DEVLET SU İŞLERİ GENEL MÜDÜRLÜĞÜ

DSİ GENEL MÜDÜRÜ

Akif ÖZKALDI

GENEL MÜDÜR YARDIMCILARI

Güven KARAÇUHA Ali Cüneyt GEREK Ömer ÖZDEMİR Döndü TATLIDİL

ETÜD ve PLAN DAİRESİ BAŞKANLIĞI

DAİRE BAŞKANI

Salim FAKIOĞLU

BAŞKAN YARDIMCILARI

M.Sait TAHMİSCİOĞLU Doç.Dr.Yakup DARAMA Ahmet ÖZBEK

Rasatlar Şube Müdürü	Ayhan AKGÖZ
Hidroloji Şube Müdürü	Miktat YAVUZ
I.Planlama Şube Müdürü	Murat HATİPOĞLU
II.Planlama Şube Müdürü	Hasan GÜLER
III.Planlama Şube Müdürü	Nedret ÜNEL
IV.Planlama Şube Müdürü	Nazmi KAĞNICIOĞLU
Tahsisler Şube Müdürü	
Çevre Şube Müdürü	Fikriye BALTACI
Tarımsal Ekonomi Şube Müdürü	Murat SAN
Toprak Drenaj Şube Müdürü	Ramazan YÜCEL
Harita Şube Müdürü	Ali ERBAŞ
Taşkın Etüdü ve Planlaması Şube Müdürü	Mehmet İNAL
Erozyon ve Rusubat Kontrol Şube Müdürü	İbrahim BİROĞLU
Su Toprak Laboratuvarı Şube Müdürü	
İhale Tatbikat Şube Müdürü	Murat ŞAYAN
Avrupa Birliği ile İlişkiler Şube Müdürü	Ayla EFEOĞLU
Uluslararası Hidrolojik Faaliyetler Şube Müdürü	
Strateji Geliştirme Şube Müdürü	Harun AKIN
İdari İşler Şefi	Resul ÖTER

AKIM YILLIĞINI HAZIRLAYAN

RASATLAR ŞUBE MÜDÜRLÜĞÜ PERSONELİ

Ayhan AKGÖZ
Şube Müdürü

Semra SEZER Matematikçi	Cemal GÜL Meteo.Müh.	Hakan AKSU Meteo.Müh.
Ali DOĞAN Meteo.Müh.	Serdar KALKAVAN Meteo.Müh.	Mehmet SOYLU Meteo.Müh.

TEKNİSYENLER

Adnan GÜLTEKİN	Canan ERDOĞDU
Cemal AYBAT	Ercan PİRDOĞAN
Erol AYDEMİR	Hakkı USLU
Hasan Hüseyin UÇGUN	Mesut İNCE
Metin ARSLAN	Mustafa CEYLAN
Mustafa KURT	Muzaffer CİĞERİM
Nazif GÜNSEL	Nermin GÜZELDEMİRCİ
Sinan TEKİN	Yıldırım TEKİNAY

AKIM YILLIĞINDAKİ VERİYİ TEMİN EDEN

DSİ BÖLGE MÜDÜRLÜKLERİ
RASATLAR BAŞ MÜHENDİSLİĞİ PERSONELİ

1.Bölge Müdürlüğü (Bursa)

Ekip Şefleri

Ertuğrul KANYILMAZ
Kemal TANKIRCI

Teknisyenler

M.Selçuk SAĞSÖZ
Halil YAVUZ
Sami SÜMER
Sefer AYDIN
Şamil VURAL
Necati YILMAZ

2.Bölge Müdürlüğü (İzmir)

Ekip Şefleri

Ekrem ÖZER
Mert Sıtkı ŞEN

Teknisyenler

Cemil GÜL
M.Akif ÖZDEN
Refai ÇELİK
Gürbüz KAMİLOĞLU
Necati ÖZMEN
Cihat ÖZKAN
Kemal GÜL
Recep HAYDARLAR
Ersan GÜVENLİ
Nesim ACAR
İbrahim GÖK
Yıldırım YILDIRIM
Mevlüt DURAN

3.Bölge Müdürlüğü (Eskişehir)

Ekip Şefleri

Erkan GÖKDAĞ
İpek ŞENER

Teknisyenler

Ali Rıza ÖZBEK
Ali ASLANTALAY
Burhan BAŞ
Salih SEZER
Cevat BEKÇİ
H.İbrahim ÇINAR
Ekrem UZUN
Ertuğrul SARIBAŞ

4.Bölge Müdürlüğü (Konya)

Ekip Şefleri

Adnan BAŞARAN
Reyhan YALÇIN

Teknisyenler

Erol BİLGE ÖZBEK
Eser SIR
İsmail MAZLUM
Enver KORKMAZ
Mevlüt ARSLAN
Süleyman ERÖZ

AKIM YILLIĞINDAKİ VERİYİ TEMİN EDEN

DSİ BÖLGE MÜDÜRLÜKLERİ
RASATLAR BAŞ MÜHENDİSLİĞİ PERSONELİ

5.Bölge Müdürlüğü (Ankara)

Ekip Şefleri

Atilla AYDOĞAN
İbrahim AKIN
Yalçın ŞAH

Teknisyenler

Özden SANGU
Mustafa AKSAKAL
Naci KARAMAN
Mehmet AKKAYA
Cemal YALABIK
Mehmet ESER
Muhsin SAYICI
Adnan SUBAŞI

6.Bölge Müdürlüğü (Adana)

Ekip Şefleri

Ali DERTSİZ
Mustafa ALKAYA

Teknisyenler

Erol BAŞDOĞAN
Bekir ÖZKUL
Serdar KILIÇ
Osman GÜL
Yüksel SAYDAM
Adem TAŞAR
Mehmet İSTANBULLU
Ahmet ŞEN

7.Bölge Müdürlüğü (Samsun)

Ekip Şefi

Nural YAKIN

Teknisyenler

Neşat KARACAİR
Ayhan ABACI
Ali ULUS
Birol ÖZKAN
Ferhan ÇAKIR
Ünal İKİZLER
Mehmet HONİ

8.Bölge Müdürlüğü (Erzurum)

Ekip Şefi

Hasan Burak YALÇIN

Teknisyenler

Atilla KÜTÜKOĞL
Ömer Faruk HAŞİMOĞLU
Recep KESKİN
Çetin LİMON
Sinan AY
Ömer TOKGÖZ
Davut SEVİLİR
Ahmet TOKDEMİR
Orhan GÖNÜLTAŞ

AKIM YILLIĞINDAKİ VERİYİ TEMİN EDEN

DSİ BÖLGE MÜDÜRLÜKLERİ
RASATLAR BAŞ MÜHENDİSLİĞİ PERSONELİ

9.Bölge Müdürlüğü (Elazığ)

Ekip Şefi
Ömer Ali
YİĞİT

Teknisyenler

Cezmi AYTEKİN	İ.Halil KILINÇ	Ercan ÖZAY	Alaaddin BAYDEMİR	Bilal DEMİR
Mustafa GÜMÜŞ	Feyyaz KARAKAYA	M.Kaya YÜCEL	Mehmet ERARSLAN	Necdet BALİ
	Selahattin BAZENCİ	Tahir ÇİĞDEM	Cezair AKÇANLI	

10.Bölge Müdürlüğü (Diyarbakır)

Ekip Şefleri

Murat TUYGU	Handan TUYGU

Teknisyenler

Ahmet Cemal ÜLKÜ	Mehmet Emin TÜFENK	Serdar BOSTAN	Remzi KORKMAZ	Kemal MALKOÇ
	Ahmet ÖNER		Abdullah ARCAGÖK	

11.Bölge Müdürlüğü (Edirne)

Ekip Şefleri

Sadettin MALKARALI	Mehmet Seren KORKMAZ

Teknisyenler

Kani AVCI	Mehmet LOMÇALI	Serkan TAŞTARLA	M.Seşçuk ÇAKIR	Emin ADA

12.Bölge Müdürlüğü (Kayseri)

Ekip Şefi
Basri
CAN

Teknisyenler

Ramazan ÖRDEK	M.Ramazan ERCİŞ	Ramazan YORULMAZ	Adnan ERCİYESLİOĞLU	Hikmet GÖKŞEN
	Mustafa YILDIRIM		Ayhan ŞAFAK	

AKIM YILLIĞINDAKİ VERİYİ TEMİN EDEN

DSİ BÖLGE MÜDÜRLÜKLERİ
RASATLAR BAŞ MÜHENDİSLİĞİ PERSONELİ

13.Bölge Müdürlüğü (Antalya)

Ekip Şefleri

Funda Oruç KOÇYİĞİT

Nilgün Temir KÖKSOY

Teknisyenler

Önder KOCA

Durmuş DURGUN

Bayram KARA

Alim KAL

Osman KADAİF

Ramazan BAŞ

Çağlar KOZCALI

Gökhan CAN

Miraç GÜNGÖR

Can EROL

İbrahim KARATAŞ

Emin HELVACI

14.Bölge Müdürlüğü (İstanbul)

Ekip Şefi

İlyas EKŞİ

Teknisyenler

Uğur TÜYSÜZ

Ziya DEMİRBAŞ

İbrahim ERAT

15.Bölge Müdürlüğü (Şanlıurfa)

Ekip Şefi

Hüseyin Sefa HIZLI

Teknisyenler

Eyüp Sabri AYDOĞDU

Mehmet Ali KOÇOĞLU

Mahmut MIZRAK

17.Bölge Müdürlüğü (Van)

Ekip Şefi

Bekir Ragıp YURTSEVEN

Teknisyenler

Metin ÇALIŞKAN

Sinan KURTULUŞ

Servet KURTBEYOĞLU

Hidayet İRİTAŞ

Sabahattin HAKTAŞ

Bayram BEGCE

AKIM YILLIĞINDAKİ VERİYİ TEMİN EDEN

DSİ BÖLGE MÜDÜRLÜKLERİ
RASATLAR BAŞ MÜHENDİSLİĞİ PERSONELİ

18.Bölge Müdürlüğü (Isparta)

Ekip Şefi
Süleyman
TOPÇU

Teknisyenler

Erdoğan YILDIZ	Uğur HEYBELİ	Mahir GÜNKAYA	Hasan METİN	Hıdır NURCAN
Mustafa ALTOK	Tamer BABALIK	Mustafa YİĞİT	İbrahim MUDUL	Mustafa ALICI
	Ali ALTINTAŞ		Necmettin GÜNASLAN	

19.Bölge Müdürlüğü (Sivas)

Ekip Şefi
Gül
ATEŞ

Teknisyenler

Rasim TANYILDIZ	Mustafa İŞBİLİR	Rasim ŞEKER	Hacı TURMUŞ

20.Bölge Müdürlüğü (Kahramanmaraş)

Ekip Şefleri

Mehmet Durmuş KEÇİK	Eser BORA

Teknisyenler

Doğan KORKMAZ	Hacı Bayram KORUCU	Hayati KAYHAN	Arif KALEBAŞI	Kazım AKIN
	Cengiz YILMAZ	Zikrulah TÜRKAN	Mehmet KENGER	

21.Bölge Müdürlüğü (Aydın)

Ekip Şefi
Mustafa
KARAÇAM

Teknisyenler

Salih ÖZKAN	Mahmut ULUDUT	Hüseyin ÜNAL	Tuğfan ÖZTÜRK	Muzaffer GÖNÜLAÇAR
Necati BEYHAN	Mustafa ŞİMŞEK	Ömer TURHAN	Mehmet ÇULHA	Erkan KARGILI
		Faruk ERTEMLİ		

AKIM YILLIĞINDAKİ VERİYİ TEMİN EDEN

DSİ BÖLGE MÜDÜRLÜKLERİ
RASATLAR BAŞ MÜHENDİSLİĞİ PERSONELİ

22.Bölge Müdürlüğü (Trabzon)

Ekip Şefleri

Alırıza AYDIN

Hayati AKYÜZ

Teknisyenler

Sabri KARA

Hayyam GENÇ

Mustafa KAVZOĞLU

Ertan ERTUĞRUL

Engin ELMAS

23.Bölge Müdürlüğü (Kastamonu)

Ekip Şefi

Erdal ARSLAN

Teknisyenler

Kemal SANCAKTAR

Abdullah HOTANOĞLU

24.Bölge Müdürlüğü (Kars)

Ekip Şefi

Murat SEZER

Teknisyenler

Efkan ÇELİK

Kubilay DAŞDEMİR

Erkan ELYAGUT

Metin POLAT

İsmail ZAMBAK

İsmail ÇELİK

Nevruz KAYAHAN

25.Bölge Müdürlüğü (Balıkesir)

Ekip Şefleri

Neşet DEMİR

Mehmet Ali AYDIN

Teknisyenler

Sinan KÜLTOZATAN

Gülin TAŞCI

Niyazi UZANMIŞ

Ali YILDIRIM

İÇİNDEKİLER

İçindekiler	IX - XXX
Kitabın İçeriği, Açıklaması ve Düzenleniş Yöntemleri	XXX - XXXIV
Su Yıllarına Göre Gözlem İstasyonları Adedi ve Akım Ölçü Sayısı Grafiği	XXXV
AGİ Akım Değerleri (Bölüm I)	1 - 781
GGİ Seviye Değerleri (Bölüm II)	783 - 787
Değerlendirmeye Alınamayan Gözlem İstasyonları (Bölüm III)	789 - 835

1.MERİÇ HAVZASI

İst.No.	Suyun Adı	İstasyonun Adı	Sayfa
1-1	Meriç N.	Kapıkule	789
1-3	Meriç N.	Kirişhane	1
1-4	Meriç N.	Eskiköy	789
1-8	Ergene N.	Lüleburgaz DDY.KÖp.	2
1-13	Hayrabolu Deresi	İnecik	789
1-20	Ergene N.	İnanlı	3
1-26	Meriç N.	İpsala Köp.	4
1-31	Soğucak D.	Soğucak	5
1-39	Poyralı D.	Poyralı	6
1-46	Hamza D.	Kocahıdır	7
1-47	Altınyazı Brj.	Göl Gözlem	789
1-52	Manika D.	K. Yoncalı	789
1-55	Provadi D.	Hasanağa Köyü	8
1-57	Meriç N.	Ferek Köprüsü	9
1-58	Çömlek D.	Çömlekkoy	789
1-61	Çeşme D.	Foyralı	789
1-62	Fişine D.	B.İsmailce	10
1-63	Ayvacık D.	Ayvacık	11
1-64	Çakmak D.	Çakmak	789
1-65	Çayır D.	Çayırköy	12
1-69	Dolap dere	İslambeyli	13
1-70	Değirmenci Göleti	Göl gözlem	789
1-71	Keramettin Göleti	Göl gözlem	789
1-72	Doğanca Göleti	Göl Gözlem	789
1-73	Dokuzdere Göleti	Göl Gözlem	789
1-74	Değirmendere	Yenice	789
1-75	Kocadere	Küçüköğünlü	789

2.MARMARA HAVZASI

2-4	Göksu D.	Şıhlar	15
2-6	Kiraz D.	Yuva Köy	16
2-10	Kocabaş Ç.	Akkayrak	17
2-15	Karasu	İnceğiz	18
2-25	B. Çekmece G.	Göl gözlem	790
2-28	Istranca D.	Karaman D.	19
2-30	Kocadere	Sölöz	20
2-31	Kara D.	Çakırca	21
2-32	Işıklar D.	Emiralı	22
2-33	Kovan D.	Emiralı	23
2-41	Yalak D.	Ayazma	24
2-47	Malava D.	Pirinçköy	25
2-52	Çınar D.	Çelikgörü	790
2-54	Alibey Brj	Göl Gözlem	790
2-55	Ozan D.	Bıçkı Dere	26
2-57	Papaç D.	Kızılağaç	27
2-59	Atikhisar Brj.	Göl Gözlem	790

İst.No.	Suyun Adı	İstasyonun Adı	Sayfa
2-62	Kavak D.	Kavak	790
2-65	Sarı Ç.	Nişankaya	28
2-66	Atıkhisar Barajı	Dolusavak	790
2-67	Göçbeyli D.	Göçbeyli	29
2-69	Kaynarca D.	Cihadiye	30
2-70	Bayram D.	Adatepe	31
2-77	Safrandere	Kurtköy	32
2-83	Kapuzlu D.	Teşvikiye	33
2-84	Kocaçay	Aşağı Çavuş	34
2-85	Kocabaş Ç.	Uzunalan	35
2-86	Atikhisar Brj.	Sol Ana Kanal	790
2-87	Atikhisar Brj.	Sağ Ana Kanal	790
2-89	K.Kumla D.	K.Kumla	790
2-92	Yaman D.	Kapaklı	36
2-94	Işıklar D.	Naipköy	37
2-98	Yulaflı D.	Alaybey	38
2-99	Y.Düzdere	Kandıra	39
2-100	Kurudere	Pargalı	40
2-101	Yılgındere	Çelebiköy	41
2-102	Kabaközdere	Kabaközköyü	42
2-104	Kumcağız D.	Kefken	43
2-105	Kovanlık D.	Boztaş	44
2-107	Kılıncı D.	Kemerburgaz	45
2-109	İznik Gölü	Göl Gözlem	791
2-116	Sarısu D.	İzzettin	46
2-117	Çakıl D.	Ahmediye	47
2-119	Velika D.	Armutveren	48
2-120	Kocadere	Çağlayık	49
2-121	Balıklı Ç.	A.İnova	791
2-123	Kocadere	Muratoba	791
2-124	İznik G.	Göl Gözlem (Boyalıca)	791
2-125	Sellimandıra D.	Gökçe Brj.GİRİŞ	50
2-126	Suludere	İhsaniye	51
2-129	Karanlık D.	Kırıklar	52
2-130	Ayna D.	Erdek	791
2-132	Kocaçay D.	Kumarlar	53
2-133	Yağcı D.	Semetler	54
2-134	Kara D.	Karadere Köyü	55
2-135	Avcı D.	Avcıköy	56
2-136	Kağıthane D.	Kağıthane	57
2-137	Kurbağalı D.	Kadıköy	58
2-138	Gönen Ç.	Bayatlar	59
2-139	Yuvacık Brj	Yuvacık	791
2-140	Yeşildere	Kalealtı	60
2-141	Değirmedere	Kocayazı	61
2-142	Türkmenli Brj.	GGİ	791
2-143	Kazandere	Küçükyayla	62
2-144	Cevizdere	Naipköy	791
2-145	Küçükköy D.	Yeşilpınar	792
2-146	Ayazağa D.	Ayazağa	792
2-147	Uludere	Umurbey Brj. Çkş.	792
2-148	Alibeyköy D.	Alibeyköy	792

3.SUSURLUK HAVZASI

3-4	Kille D.	Devecikonağı	792
3-8	Madra Ç.	Güngörmez	63
3-13	Kille D.	Ikizcetepeler	64
3-17	Bedir Ç.	Çavdarhisar	792
3-18	Kızık S.	Ağrı Köyü	65
3-20	Koca D.	Akçaşehir	792
3-21	Üzümcü S.	Küçükbostancı	66

İst.No.	Suyun Adı	İstasyonun Adı	Sayfa
3-24	Madra Ç.	Ayaklı	67
3-25	Cüneyt Ç.	Cüneyt Köp.	68
3-27	Gölbaşı Gölü	Çıkış	792
3-28	Aksu D.	Gölbaşı Göl. Giriş	792
3-29	Deliçay Kan.	Panayır Köprüsü	793
3-34	Simav Ç.	Osmanlar Köp.	69
3-36	Çaygören Brj.	Göl Gözlem	793
3-37	Gölbaşı Gölü	Göl Gözlem	793
3-38	Kırkpınarlar D.	Uludağ	793
3-41	Çaygören B.	Dipsavak	793
3-42	Çaygören B.	Anakanal	793
3-43	Simav Ç.	Çaygören Brj.Dolusavak	70
3-44	Selahattin Saygı Brj	Giriş	71
3-47	Manyas G.	Göl Gözlem (Ergili Reg.)	793
3-49	Cuma D.	Cuma Yeri	793
3-51	Köteyli D.	Dereboğazı	72
3-52	Dursunbey D.	Sinderler	73
3-54	Nilüfer Ç.	Güneybayır	74
3-56	Sultaniye D.	Sultaniye	75
3-64	Gölecek D.	Gölecek	76
3-67	Mürvetler D.	Sol kanal	77
3-73	Simav Ç.	Gökçedağ	793
3-75	Nülüfer Ç.	Doğancı Brj.Çıkı	793
3-76	Kara Dere	Dadalar	78
3-77	Doğancı Brj.	Göl Gözlem	794
3-79	Kuruçay Göleti	Göl Gözlem	794
3-80	Kayaboğazı Brj.	Göl Gözlem	794
3-81	Mürvetler D.	Mürvetler(01-02)	79
3-82	Kocadere	Keçiler	80
3-83	Kocadere	Esatlar	81
3-84	Değirmendere	Keşbükü	82
3-85	Yaylacık D.	İnegazı	83
3-86	Kocadere	Adalı	84
3-87	Kocabük D.	Yeşilova	794
3-89	Orhaneli Ç.	Çaltıbük	85
3-90	Orhaneli Ç.	Deliballılar	86
3-93	Manyas Gölü	Göl Gözlem (Gölyaka)	794
3-95	Kabaklar D.	Hasanlar	87
3-96	Oben D.	Okçular	88
3-97	Çavdar Hisar B.	Göl Gözlem	794
3-100	Susurluk Ç.	Canbolu	794
3-102	Orhaneli Ç.	Çayören	89
3-104	Değirmendere	Doğanlar	90
3-108	Karadere	Paşalar	794
3-112	Eğri D.	Doğruöz	794
3-114	Ulubat G.	Eskikaraağaç	794
3-115	Karadere	İsmetpaşa	91
3-117	Bağlar Yanı	Arapşah	92
3-118	Karaerik D.	Domur	93
3-119	Değirmendere	Örenli	795
3-120	Kayadere	Yeşilköy	94
3-122	Yenice Göleti	Göl Gözlem	795
3-123	Çerte Göleti	Göl Gözlem	795
3-124	Manyas G.	Eskibalıkhane	795
3-125	Emet Ç.	Düğüncüler	795
3-126	Söğütalan D.	Güller	795
3-127	Uluabat G.	Göl Gözlem (Halilbey)	795
3-128	Simav Ç.	Kadıköy	795
3-129	Dursunbey Ç.	A.Yağcılar	95
3-130	Killi Ç.	Sarı Çayır	96
3-132	Çaylak D.	Çaylak	97
3-133	Narlı D.	Narlı D.Köprüsü (2005)	98-99

İst.No.	Suyun Adı	İstasyonun Adı	Sayfa
3-135	Donbay D.	Dedektaşı	100
3-136	Koca Ç.	Kayaca	101
3-137	İkizcetepeler Brj.	Göl Gözlem	795
3-139	Nilüfer Ç.	Nilüfer Brj Giriş	102
3-140	Umurlar Ç.	Yusufçam	103
3-141	Eğri D.	Gölcük(Sındırgı)	104
3-142	Uzundere	Arttıranlar	795
3-143	Taşkışla D.	Arttıranlar	796

4.KUZEY EGE HAVZASI

4-13	Madra Ç.	Selimiye	105
4-16	Karadere	Bahadınlı	106
4-17	Karınca D.	Reşitköy	107
4-21	İlyas Ç.	Çaltıköprü	108
4-26	Yortanlı D.	Paşaılıcası	109
4-28	Tuzla Ç.	Ayvacık	110
4-31	Eybek Ç.	Eybek	111
4-32	Tuzla Ç.	Korubaşı	112
4-35	Kocdere	Misvak	796
4-36	Zeytinli D.	Zeytinli	113
4-38	Karakoc D.	Bogazbahce	796
4-39	Bezirganlar Ç.	Kayser	114
4-41	Ilıca D.	Zeytinli	796
4-42	Manastır Ç.	Kavlaklar	796
4-43	Candere	Kınık	115
4-44	Geyikli D.	Mazılı	796
4-45	Himmet D.	Çıtak	116
4-46	Akçay D.	Aydıncık	117
4-47	İnönü D.	İnönü	118
4-48	Bakırçay	Eğrigöl	797
4-49	Bakırçay	Göçbeyli	797
4-50	Hasandere	Çamavlu	797
4-51	Cumalı D.	Cumalı	119
4-52	Kışla D.	Dereobası	120
4-53	Ilıca D.	Sarıcalar	121
4-54	Koca D.	Musaçalı	122
4-55	Havran Ç.	Havran Brj.Çkş.	797

5.GEDİZ HAVZASI

5-5	Marmara gölü	Göl Gözlem	797
5-7	Marmara gölü	Reg. Çıkış	797
5-15	Medar Ç.	Medar Köprüsü	797
5-18	Nif Ç.	Çiçekli	123
5-21	Tabak D.	Çaltılı	797
5-25	Gediz N.	Muradiye Köp.	798
5-26	Sarma Ç.	Sarma	124
5-28	Gördes Ç.	Hacıhıdır	798
5-31	Alaşehir Ç.	Taytan Köp.	798
5-33	Gediz N.	Urganlı	798
5-34	Gordes Ç.	Maden Çeşmesi	798
5-35	İm D.	Güneşli	125
5-38	Nif Ç.	Hacıaliler	798
5-39	Ahmetli Ç.	Dereköy	126
5-43	Cemal D.	Kayganlı	127
5-44	Demir büken D.	Başlamış	128
5-45	Gümele Göleti	Göl Gözlem	798
5-46	Combulat D.	Gümele	798
5-48	Değirmen D.	Doğanlar	129

İst.No.	Suyun Adı	İstasyonun Adı	Sayfa
5-49	Kayacık D.	Çağlayan	130
5-50	Ayan D.	Çamurköy	131
5-51	Gölcük G.	Göl Gözlem	798
5-52	Karanohut dere	Karanohut	132
5-53	Zeytin Ç.	Osmaniye	133
5-54	Delice D.	Çamönü	799
5-55	Girlevik D.	Akçapınar	134
5-56	Kavaklı D.	Dereköy	135
5-57	Asmak Ç.	Savram	799
5-58	Demirköprü	Göl Gözlem	799
5-59	Gediz N.	Demirköprü Brj.Çıkış	799
5-60	Gediz N.	Hamidiye Köprüsü	799
5-62	Ağıllıboğazı D.	Çanakçı	799
5-63	Armutlu D.	Armutlu	136
5-64	Diken D.	Sarıburun	137
5-65	Geçtin D.	Doğanpınar	138
5-66	Selendi D.	Selendi	139
5-67	İmren D.	Ulucak	140

6.KÜÇÜK MENDERES HAVZASI

6-11	Rahmanlar Ç.	Bebekler	141
6-13	Falaka Ç.	Falaka	799
6-18	Arapastan D.	Davutlar	799
6-19	Elekçi D.	Davutlar	142
6-22	Hırsız D.	Baraj Giriş	800
6-24	Gelinalan D.	Seferihisar	143
6-25	Uladı Ç.	Yakapınar	144
6-26	Pirinçci Ç.	Bademli	145
6-27	Uluca D.	Ergenli	146
6-28	Derince D.	Küçükbahçe	147
6-29	Camiboğazı D.	Karareis	148
6-30	K.Menderes N.	Ödemiş	800
6-31	K.Menderes N.	Mahmutlar reg.	800
6-32	K.Menderes N.	Selçuk	800
6-33	Kiraz Ç.	Kiraz	149
6-34	Kızıkkaya D.	Yenişehir	150

7.BÜYÜK MENDERES HAVZASI

7-2	Işıklı Gölü	Göl Gözlem	800
7-3	Kufi Ç.	Işıklı Köp.	151
7-7	Çürük S.	Böceli Reg	800
7-8	Gökpınar Ç.	Akhan Reg. Giriş	152
7-9	Çine Ç.	Çakırbeyli Köp.	153
7-10	Dinar S.	Irgıllı Reg. Çıkış	154
7-14	İkiz D.	Dereağzı	155
7-15	Tabakhane D.	Tesip Bendi	156
7-24	Bafa Gölü	Göl Gözlem	800
7-26	Dinar S.	Irgıllı Sul. Kan.	157
7-30	Köşk D.	Mezeköy	158
7-32	B.Menderes N.	Nazilli Köp.	159
7-35	Çine Ç.	Söğütlü	800
7-39	Kapız Ç.	Alangüllü	800
7-49	Karadirek Ç.	Başağaç	800
7-52	Gömü D.	Çevre Pınar	160
7-53	Işıklı Pınarı	Tahliye Kan.	800
7-54	Işıklı Pınarı	Sulama Kan.	801
7-59	Çürük Suyu	Yukarı Şamlı Köp.	161
7-61	Dandalas Ç.	Beşdeğirmenler	162

İst.No.	Suyun Adı	İstasyonun Adı	Sayfa
7-62	B.Menderes N.	Koçarlı Köp.	801
7-65	B.Menderes N.	Adı Güzel	163
7-67	Çapalı Gölü	Göl Gözlem	801
7-71	B.Menderes N.	Y Seyitler	164
7-75	Kumalar Ç.	Karakuyu	165
7-79	Girme D.	Girme	166
7-81	B.Menderes N.	Saray Köp.	167
7-82	Madran Ç.	Kasar	168
7-83	Yeni D.	Çalıköy Köp.	169
7-86	Topçam B.	Göl Gözlem	801
7-87	Kestel D.	Kızılca	170
7-93	Korkoz D.	Değirmenburnu	171
7-96	Gevenez D.	Gevenez	172
7-97	Elekçi D.	Madamlar	173
7-98	Sıra İnlerdere	Bayır	174
7-99	Alişardere	Alişar	175
7-100	Delice D.	Kırıklar	176
7-103	Sarı Ç.	Bağarası	177
7-106	Emir Ç.	Çambaşı	178
7-107	Cılımbız D.	İncirliova	801
7-108	Karsın D.	Köprüalan	801
7-109	Yalkı D.	İncirliova	801
7-111	Kestel D.	Kızılca Baraj yeri	802
7-112	Çapalı Gölü	Regülatör Çıkışı	802
7-114	Deliçay	Kazandere	802
7-115	B.Menderes N.	Yenice Reg.	179
7-116	Kemer Brj	Göl Gözlem	802
7-117	Adıgüzel Brj	Göl Gözlem	802
7-118	Yaylakavak Brj	Göl Gözlem	802
7-119	Çapalı G.	Göl Gözlem	802
7-120	Çapalı G.	Çıkış	180
7-121	Kayran D.	Pamukören	181
7-122	Banaz Ç.	Banaz	182
7-124	Avşar Ç.	Haydarlı	183

8.BATI AKDENİZ HAVZASI

8-6	Kara Göl	Göl Gözlem	783
8-9	Kireniş Ç.	Çakır Köp.	185
8-18	Ballık D.	Ballık Boğazı	186
8-19	Sarı Ç.	Kocakavak	187
8-28	Esen Ç.	Yapılar	802
8-49	Başgoz Ç.	Gökbük	188
8-54	Kemer D.	Osman Kalfalar	802
8-60	Hamzabey D.	Gökçeler	802
8-61	Mumur D.	Mumur	189
8-63	Alakır Brj	Göl Gözlem	784
8-66	Gölhisar Gölü	Göl Gözlem	803
8-67	Söğüt Gölü	Çıkış	190
8-70	Horzum Ç.	Yapraklı	191
8-71	Ağaova D.	Asibucak	803
8-72	Dalaman Ç.	Meşebükü	803
8-73	Dalaman Ç.	Narlı	192
8-74	Dalaman C.	Sami Saydam	803
8-75	Değirmen D.	Hisarardı	803
8-78	Akçay Ç.	Gömbe	193
8-79	Aksu D.	Çamköy	194
8-81	Arslanlı Ç.	Sorkun Köp.	195
8-83	Dargas D.	Lengüme	196
8-84	Değirmen D.	Sodaköy	197
8-85	Nanman Ç.	Doğuşbelen	803
8-87	Değirmen D.	Karadan	198

İst.No.	Suyun Adı	İstasyonun Adı	Sayfa
8-89	Kargı Ç.	Yanıklar	199
8-91	Esen Ç.	Örenköy Reg.	200
8-92	Bayır Ç.	Gökçeburun	201
8-94	Değirmendere	Dereköy	202
8-95	Mürmür D.	Yılmazlı	203
8-96	Değirmen D.	Milas	204
8-97	Derince D.	Derince	803
8-98	Esence D.	Kızılyıkık	804
8-99	Kondak Ç.	H. Ahmetler	205
8-100	Karabalçık D.	Çobanhisar	206
8-101	Kocaçay D.	Epçe	207
8-103	Dalaman Ç.	Çamköy	208
8-104	Değirmendere	Akalan	209
8-105	Yavan olukdere	Y.Dodurga	804
8-106	Çatal olukdere	Karaçulha	210
8-107	B.Dere	Karahasanlı	804
8-108	Seki Ç.	Gaçakboğazı	211
8-109	Geyık S.	Nifköyü	804
8-110	Elmalı D.	Nifköyü	804
8-111	Alanlı D.	Nifköyü	804
8-112	Kanlıgöl D.	Karacahisar	212
8-114	Geyik B.	Göl Gözlem	804
8-115	Kocaalan D.	Marmaris	804
8-118	Karadere	Hisarönü	804
8-119	Mumcular Brj.	Göl Gözlem	805
8-120	Sarıçay	Geyik Brj.	805
8-121	Batış Dere	Karaova	805
8-122	Yapraklı Gölü	Göl Gözlem	805
8-128	Oluk D.	Toptaş	805
8-132	Çayboğazı Brj.	Göl Gözlem	785
8-133	Çavdır Barajı	Göl Gözlem	805
8-134	Çaydere	Beşikci Kumluca	213
8-135	Karabayır D.	Karabayır	214
8-140	Kargacık D.	Köyceğiz	215
8-141	Fetaş	HES Giriş	805
8-142	Gerin D.	Bozalan	805
8-143	Kocaçay	Ören	216
8-144	Akdere	Ören Acıpayam	217

9.ANTALYA HAVZASI

9-2	Yenice Ç.	Zindan Boğ.	219
9-6	Dim Çayı	Sağ S.S.K.	220
9-9	Eğridir Gölü	Göl Gözlem	805
9-11	Korkuteli Ç.	Salamur Bağ.	221
9-13	Dim Çayı	Reg Çıkış	222
9-16	Kovada Gölü	Çıkış	223
9-17	Kovada GÖlü	Göl Gözlem	805
9-31	Karaman Ç.	Kapuz Sulama kn Çıkış	224
9-34	Küçükaksu	Gediz	225
9-39	Onaç Brj	Giriş	226
9-42	Ağlasun Ç	Ağlasun	227
9-45	Onaç Brj	Göl Gözlem	806
9-56	Düden Ç.	Reg.Mansap	228
9-57	Hoyran D.	Gökçeli	229
9-59	Hoyran Gölü	Göl Gözlem	806
9-60	Çaydere G.	Göl Giriş	230
9-65	Yalvaç Sucullu Brj.	Göl Giriş	231
9-67	Karpuz Ç.	Uzunlar	232
9-68	Kargı Ç.	Türkler	233
9-71	Korkuteli Brj.	Göl Gözlem	786

İst.No.	Suyun Adı	İstasyonun Adı	Sayfa
9-73	Pupa Ç.	Senirkent	806
9-75	Gelendost D.	Gelendost	234
9-84	Oba Ç.	Kadıpınar	235
9-86	Aksu D.	Belence	236
9-88	Değirmendere	Sütçüler	237
9-89	Değirmendere	Selimler	238
9-90	Sorkun D.	Ananas	806
9-91	Kırkgözler	İsale Kanalı	239
9-95	Çandır Ç.	Yemişli Pınarı	240
9-96	Karacaören Barajı	Göl Gözlem	806
9-98	Aksu Ç.	Karsı	806
9-100	Başak D.	Yanıkköy	241
9-101	Köprü ç	Karakaya	242
9-104	Beyhasan D	Ağırtaş	243
9-111	Doyuran D.	Doyuran	244
9-113	Eğridir G.	Göl Gözlem	806
9-114	Kızlar D.	Yavrudoğan	245
9-116	Naras D.	Şişeler Köyü	246
9-117	Alıcı D.	Gündoğmuş	247
9-118	Boğalak D.	Taşagil	248
9-120	Giren D.	Ormana	249
9-121	Boyalı Ç.	Doyran	250
9-122	Sağarin D.	Çardak	251
9-123	Çukurca Ç.	Narlı	252
9-124	Koca D.	Akbaş	253
9-125	Kurupınar D.	Küçükköy	254
9-126	Asar D.	Küçükköy	255
9-127	Delice Ç.	Yeniköy	256

10.BURDUR GÖLLER HAVZASI

10-7	Değirmenler D.	Karamanlı Brj.Çıkış	806
10-8	Karataş Gölü	Göl Gözlem	806
10-13	Bozçay	Yazıköy	257
10-21	Karaman Brj.	Göl Gözlem	807
10-23	Karaman Brj.	Giriş	258
10-27	Buğdüz D.	Buğdüz	259
10-32	Değirmen D.	Başmakçı	260
10-33	Buğdüz D.	Buğdüz	261
10-34	Baynaz D.	Bayramlı	807

11.AKARÇAY HAVZASI

11-1	Eber G.	Eber G. Çıkış	807
11-2	Adıyan S.	Ortaköy	263
11-3	Akşehir Gölü	Göl Gözlem	807
11-4	Eber Gölü	Göl Gözlem	807
11-5	Seyitler Brj.	Göl Gözlem	807
11-6	Seyitler Brj.	Cıkış	807
11-9	Selevir Brj.	Göl Gözlem	807
11-11	Karamık Gölü	Göl Gözlem	807
11-12	Selevir Brj	Çıkış	807
11-13	Kalı Ç.	Selevir Brj. Giriş	264
11-15	Engilli D.	Cankurtaran	265
11-17	Araplı D.	Köprülü	266
11-20	Akarçay	Akdeğirmen	267
11-21	Çay D.	Çay	268
11-22	Değirmen D.	Özburun	269
11-23	Eber Gölü	Giriş	270
11-24	Kuruçay	Sincanlı	807

12.SAKARYA HAVZASI

İst.No.	Suyun Adı	İstasyonun Adı	Sayfa
12-4	Porsuk Brj.	Göl Gözlem	808
12-6	Kargı S.	DDY Durağı	808
12-10	Çubuk 1. Brj.	Göl Gözlem	808
12-17	Kızılcahamam D.	Mandıra	271
12-33	Porsuk Ç.	Porsuk Çiftliği	272
12-34	Porsuk Brj.	Çıkış	808
12-49	Kureyşler S.	Kureyşler	273
12-54	Porsuk Ç.	Esenkara	274
12-55	Murat Ç.	Akçaköy	275
12-63	Uludere	Uluçayır	276
12-75	Sirkeli S.	Karşıyaka	277
12-83	Ravlı D.	Ravlı	278
12-91	Göynük S.	Kaşıkçı	279
12-93	Köker Ç.	Eyice	280
12-96	Bayındır Brj.	Göl Gözlem	808
12-97	Çubuk II. Brj.	Göl Gözlem	808
12-99	Sey D.	Güven	808
12-101	Kargın D.	Derivasyon Kan.	808
12-102	Kargın Brj.	Göl Gözlem	808
12-103	Hızarlı D.	Reg. Çıkış	808
12-122	Kurtboğazı Brj.	Göl Gözlem	809
12-123	Enne Brj.	Göl Gözlem	809
12-126	Mera Ç.	Pazar Yol Ayrımı	281
12-128	Ova Çayı	Reg.Derv.Kn	282
12-129	Çubuk Ç.	Yenice	283
12-133	Sapanca G.	Göl Gözlem	809
12-135	Cerrah D.	Cerrah	284
12-136	Mudurnu S.	Gebeş	285
12-138	Sırcasaray S.	Yeşilöz	286
12-145	Dodurga Brj.	Göl Gözlem	809
12-146	Göynük S.	Yeniköy	287
12-147	Pazar D.	Pazar	288
12-149	Dodurga Brj.	Çıkıs	809
12-150	Kocadere	Ömerköy	289
12-152	Kokar Ç.	Beşkarış	290
12-153	Göksu N.	Boğazköy	291
12-155	Akça S.	Ortaköy	292
12-156	Bedre S.	İsaören	809
12-159	Gökpınar S.	Aydınlı	293
12-160	Söğüt D.	Küre	294
12-162	Kaymaz Brj.	Göl Gözlem	809
12-164	Boğaz D.	Mahmudiye	295
12-167	Papaz D.	Ahılar	296
12-169	Söğüt Brj.	Göl Gözlem	809
12-170	Sarısu	Kandilli	297
12-171	Sarısu	Yenidodurga	298
12-172	Sarısu	İnönü	299
12-173	Porsuk	Gökçekışık	809
12-175	Kocadere	Akıncılar	300
12-176	Akgöl Çıkışı	Küçükhasan Köp	301
12-177	Hocaköy D.	Hocaköy	302
12-178	Hanköy	Çifteler	809
12-179	Kunduzlar Brj.	Göl Gözlem	809
12-181	Porsuk Ç.	Çalca	303
12-182	Pürtek D.	Memik	304
12-183	Keçeliözü D.	Göknebi	810
12-184	Kunduzlar Brj.	Baraj Çıkışı	305
12-185	Akın D.	Gemiş	306
12-186	Çark S.	Sapanca G.Reg.Çık.	307
12-187	Çamlıdere G.	Göl Gözlem	308

İst.No.	Suyun Adı	İstasyonun Adı	Sayfa
12-188	Nal D.	Yakapınar	308
12-189	Suvari Ç.	Zeyde	309
12-192	Çatören Brj.	Çıkış	310
12-193	Balık boğ	Kırka	311
12-194	Harami D.	Karaören	312
12-195	Çatören Brj.	Göl Gözlem	810
12-197	Darıçayır	Karapınar	313
12-198	Yırtmaçdere	İnekciköy	810
12-202	Sapanca G.	Göl Gözlem (Uzunkum)	810
12-205	Kayı Göleti	Dolusavak Çıkış	314
12-206	Sabuncu D.	Kurtköy	810
12-208	Budaklar D	Akmeşe	315
12-209	Dedebağ D.	Nasrettin Hoca	810
12-210	Akçay D.	Dogancılar	810
12-215	Porsuk Ç.	Parsibey	811
12-218	Kocadere	Dokuzlukköy	316
12-219	Anadere	Şahtımarı	317
12-220	Kemaliye	Değirmendere	811
12-222	Eğrekkaya Brj.	Göl Gözlem	811
12-223	Ankara Ç.	Sarıoba Köp.	811
12-224	Akmeşe D.	Dereköy	318
12-225	Değirmendere	Gündüzler	319
12-227	Çarşamba D.	Hisarcık	320
12-228	Gürleyik D.	Dereköy	321
12-229	Uludere	Karapürçek	811
12-230	Karakaya D.	Doğantepe	322
12-231	Kocadere	Fethiye	811
12-232	Karlan D.	Haccağız	323
12-234	Meşeli D.	Beşevler	811
12-235	Değirmendere	Dudaş	324
12-236	Göçük D.	Beyazaltın	811
12-238	Ankara Ç.	Eserkent	325
12-239	Akyar B.	Göl Gözlem	812
12-240	İlhan Ç.	Bayat Köyü	326
12-241	Asartepe Brj	Göl Gözlem	812
12-242	Mera Ç.	Uğurlu	327
12-243	Kara D.	Endil Boğazı	328
12-244	Kirmir Ç.	Yeşilöz	329

13.BATI KARADENİZ HAVZASI

13-01	Eflani Gölü	Göl Gözlem	812
13-08	Mudurnu Ç.	Akkaya	331
13-14	Ulus Ç.	Celalihan	812
13-15	Devrekani Ç.	Cürümören	332
13-21	Devrekani D.	Çorbacı	333
13-22	Akhasan D.	Akhasan	334
13-27	Gölköy Brj	Göl Gözlem	812
13-28	Yeniçağa Gölü	Göl Gözlem	812
13-32	Aksu Ç.	Dere Evi	335
13-33	K. Melen D.	İgn5eler	336
13-34	Hasanlar Brj.	Göl Gözlem	812
13-35	Hasanlar Brj.	Çıkış	812
13-36	Hacılar D.	Yalaközü	337
13-37	Eflani S.	Çevrik Köp.	338
13-38	Karadere	Kırık	339
13-39	Kocanaz D.	Boğaz Köy	340
13-40	Gerede S.	Bahçedere	341
13-41	Filyos Ç.	Balıkısık	342
13-42	İhsaniye D.	İhsaniye	343
13-44	Bolu D.	Devrek	344

İst.No.	Suyun Adı	İstasyonun Adı	Sayfa
13-45	Ulus D.	Yağbaşlar	345
13-46	Markosa D.	Salur Köp.	346
13-47	Dereköy D.	Yüzbaşı Pınarı	347
13-48	Alatlı Ç.	Ulukum	348
13-49	Arıt Ç.	Darıören	349
13-50	İspa D.	Samlıoğlu	350
13-52	Kocaırmak Ç.	Cide	351
13-53	Araç Ç.	Kayaboğazı	352
13-55	Karacasu	Kuyumculuköy	353
13-59	B.Melen	Uğurlu köyü	354
13-60	Başköy D.	Başköy	355
13-61	Araç Ç.	Araç	356
13-62	Araç Ç.	Karıt	357
13-63	Soğanlı Ç.	Karabük	358
13-64	Gerede Ç.	Bayramören	359
13-65	Büyük Ç.	Köplüce Köprüsü	360
13-66	Asar S.	Kaynaşlı	812
13-67	Devrek Ç.	Köprübaşı	812
13-68	Abant D.	Akçaalan	361
13-70	Hizar D.	Bayramışlar	362

14.YEŞİLIRMAK HAVZASI

14-6	Ladik Gölü	Göl Gözlem	812
14-11	Ladik Gölü	Reg.Çıkış Ayağı	812
14-14	Kürtün Ç.	Ahullu	363
14-23	Mecitözü S.	Kaleboğazı	364
14-24	Deliçay	Mehmetler	365
14-33	Kosmasat D.	Özbeyli	366
14-50	Dövenci D.	Fidanlık	367
14-62	Sarısu D.	Artova	368
14-64	Aksu D.	Gökçe	369
14-75	Söğütözü D.	B.Sögütözü	813
14-80	Gündelen D.	Kızıllı	370
14-81	Dereçam D.	Güven Brj. Yeri	371
14-104	Ahiilyas S.	Evciyenikışla	372
14-106	Alpu D.	Alpu Dere Köy	373
14-109	Sadah D.	Çalarlar	813
14-110	Alaca B.	Göl Gözlem	813
14-112	Köse D.	Köse	374
14-115	Çorum Brj.	Göl Gözlem	813
14-117	Çilkoru D.	Gökdere	375
14-119	Dereköy D.	Sulusaray	376
14-121	Karakuş Ç.	Kevgir kalesi	377
14-122	Karakuş Ç.	Gökçebayır	378
14-125	Tersun D.	Y.Tarsun	379
14-126	Cevizlik D.	Erenkaya	380
14-127	Uluşiran D.	Erenkaya Köyü	381
14-130	Köröğlu D	Refahiye	813
14-131	Ilgar D	Refahiye	813
14-133	Kanlı D.	Pamuklu	382
14-135	Alaca Irmagı	Dereyazı	383
14-137	Acıpınar D.	Doğanşar	384
14-140	Ağlamış D.	Çivril Köyü	385
14-141	Beylik D.	Yeşilöz	813
14-142	Özderesi	Çineköyü	813
14-143	Erikli Deresi	Türk Derbentli Köyü	814
14-144	Değirgen D.	Akarçay	814
14-145	Avcıdere	İverönü	386
14-146	Çilkoru D.	Musullu	387
14-149	Hular D.	Çamağızı	814

İst.No.	Suyun Adı	İstasyonun Adı	Sayfa
14-152	Yenihayat B.	Göl Gözlem	814
14-154	Bahçebaşı D.	Göçenli	814
14-157	Yeşilırmak	Pazar Köp.	388
14-158	Değirmendere	Ziyaret br	814
14-159	Fındık D.	Daldere	389
14-160	Silisözü D.	Mertekli	815
14-161	İshak D.	Çizözü	390
14-162	Yeşilırmak D.	Kozlu	391
14-163	Tahtalı D.	Eşmebaşı	392
14-164	Çobanlı D.	Günalan	393
14-165	Akınoğlu D.	Özbayraklı	394

15. KIZILIRMAK HAVZASI

15-10	Boğazlıyan Ç.	Yeşilhisar	395
15-15	Dündarlı S.	Hacıbeyli	396
15-17	Develi S.	Gedine	397
15-20	Balık Gölü	Göl Gözlem (Yörükler)	815
15-26	Engiz D.	Ballıca	398
15-39	K**ozayağı** D.	K**ozayağı**	399
15-54	Büyük Kanak Ç.	Kadılı	400
15-55	Sarıkaya S.	Kadılı	401
15-56	Eğriöz D.	Sorgun	402
15-66	Yozgat Ç.	Yukarıelmahacılı	403
15-69	Musabeyli D.	Musabeyli	404
15-70	İnandık D.	Arifoğlu	405
15-74	Kamerözü S.	Gündüzlü	406
15-78	Başveren S.	Terzili	407
15-91	Karamuk D.	Budaklı	408
15-92	Eşe D.	Vakfıbelveren	409
15-93	Devreş Ç.	Çukurca	410
15-95	Taretözü D.	Yeşilyazı	411
15-98	Söğütözü D.	Yuva	412
15-99	Kestavan Ç.	Sarıoğlan Çif.	413
15-107	İçin D.	Yuva	414
15-108	Kaleycik D.	Doyduk	815
15-112	Değirmen D.	Karaca Ören	415
15-115	Söğütözü D.	Tahtaköprü	416
15-117	Kızılırmak	Ahmethacı	417
15-126	Akdere	Oğulcuk	418
15-131	Bağırganözü D.	Bahaddin	419
15-133	Terme Ç.	Tüney	420
15-136	Yenice D.	Tekkeyenicesi	421
15-137	Yusufözü D.	Büyükincirli	422
15-152	Arasözü S.	Çoğun Brj. Giriş	423
15-153	Yeşilhisar D.	Akköy	424
15-164	Kızılırmak N.	Hüseyinli	425
15-167	Sarımsaklı D.	Sarımsaklı Brj. Giriş	426
15-168	Hasbek S.	Hasbeg	427
15-172	Sarımsaklı D.	Ambar Reg.	428
15-177	Terme Ç.	Koyunbaba	429
15-180	Kızılırmak N.	Oğlakpınarı	430
15-182	Hösür D.	Bozkır Brj. Giriş	431
15-185	Yıldız I.	Zengi	432
15-190	Cendereözü D.	Şahinoğlu	815
15-195	Balaban Ç.	Kuşçuali	433
15-206	Arsızözü	Uzunlu Brj.Giriş	434
15-208	Değirmenözü S.	Değirmenözü	815
15-216	Kötüdere	B.Taşlık	435
15-217	Koru D.	Fehimli Brj. Giriş	815

İst.No.	Suyun Adı	İstasyonun Adı	Sayfa
15-220	Yahyalı S.	Drenaj Kanal Giriş	436
15-224	Celep D.	Ersil	437
15-225	Daday Ç.	Hasköy	438
15-226	Daday Ç.	Goncalar	439
15-227	Karadere Ç.	Deliler	440
15-230	Güldürcek G.	Göl Gözlem	816
15-233	Yahyalı S.	Yahyalı	441
15-236	Akçakışla D.	Bozkurt	442
15-243	Kolaz Ç.	Kalebağı	443
15-249	Kanak Ç.	Yahyasaray Brj. Giriş	444
15-254	Kaymal D	Kurusaray	445
15-260	Kutanözü D.	Şarkışla	446
15-261	Dumanlı Ç.	Olukman	447
15-262	Gökdere	Kurtlapa	448
15-264	Kırıközü D.	Çukur	449
15-265	Gecmişdere	Yusufoğlan	450
15-266	Oyrat D.	Oyrat	451
15-268	Yusufoğlan D.	Yusufoğlan	452
15-272	Kuzucağın D.	Mestar	453
15-273	Köklüyurt D.	Baltalar	454
15-275	Pınarbaşı	Çepni	455
15-276	Karaboğaz D.	Şenyurt	456
15-277	Karanlık D.	Örenlice	457
15-278	Sokuözü D.	Çağlayan	458
15-282	Çoruhözü D.	Balişeyh	459
15-283	İslim D.	Hacıali	460
15-284	Kanaközü D.	Cemel	461
15-285	Bakırçay	Meryemdere	462
15-286	Budaközü D.	Kırankışla	463
15-287	Eğinoğlu D.	İncesu	816
15-288	Arifegazili D.	Arifegazili	464
15-289	Göksu D.	Eğerli	465
15-290	Kızılırmak N.	Dikmencik	466
15-292	Özdere	Felahiye	467
15-293	Çorak D.	Yukarısarıkaya Göl G.	816
15-294	Özdere	Hazarşah	468
15-295	Hacılar D.	Beyköy	469
15-296	Asacak D.	Gevrek	470
15-297	Karasu	Molu HES	816
15-298	Yoncalık D.	Eyneli G.	471
15-299	Kuru D.	Armutlu	472
15-300	Tatlı D.	Karacaören	473
15-301	Göynük D.	Hayranlı	474
15-302	Alkaya D.	Hayranlı	475
15-303	Kışla D.	Kuşçu	476
15-304	Geven D.	Karataş	477
15-306	Yıldız I.	Ali Ağılı	478
15-307	Yıldız I.	Yukarı Yıldızlı	816
15-308	Acıözü D.	Tayip	479
15-309	Seyfe G.	Göl Gözlem	816

16. KONYA KAPALI HAVZASI

16-1	Beyşehir Kan.	İncesu	816
16-3	Çarşamba S.	Mavi	481
16-13	Şarkikaraağaç S.	Çeltik Köp.	482
16-14	Soğuksu	Yeşildağ	483
16-15	Üstünler D.	Üstünler	484
16-16	Çavuşcu Gölü	Göl Gözlem	816
16-28	İbrala S.	Nalama Çif.	485

İst.No.	Suyun Adı	İstasyonun Adı	Sayfa
16-42	Sille Brj.	Göl Gözlem	816
16-43	Ayrancı Brj.	Göl Gözlem	817
16-45	Apa Brj.	Göl Gözlem	817
16-47	Mamasın Brj.	Göl Gözlem	817
16-48	Mamasın Brj.	Çıkış	486
16-50	Obruk Gölü	Göl Gözlem	817
16-52	Timraş Obruğu	Göl Gözlem	817
16-62	Hotamış Gölü	Göl Gözlem	817
16-66	Gebere Brj.	Çıkış	487
16-67	Gebere Brj.	Göl Gözlem	817
16-72	Altınapa Brj.	Çıkış	488
16-73	Altınapa Brj.	Göl Gözlem	817
16-76	Gümüşler Brj.	Göl Gözlem	817
16-77	Gümüşler Brj.	Çıkış	489
16-78	Superta Ç.	Taşağıl (Suğla Giriş)	490
16-80	Karasu	Demirci	491
16-81	Çığıl D.	Derivasyon Kn.	492
16-87	Ayrancı S.	Kavaklık	493
16-88	Gödet Ç.	Fisandon	817
16-89	Uzandı D.	Kırkpınar Köp.	494
16-92	Kale Reg.	Zaferiye Köp.	495
16-94	Gümüşler Brj.	Giriş	496
16-95	Apa Brj.	Çıkış	497
16-96	Apa Brj.	Alkaran	498
16-98	Melendiz S.	Selime	499
16-100	Meram Ç.	Küçükmuhsine	500
16-101	Çavuş D.	Aşağıesence	501
16-102	Ayrancı Brj.	Çıkış (Fidanlık)	817
16-104	Sarısu	Eğikler	502
16-109	Çavuşçu Göl Çıkışı	Orhaniye Köp.	503
16-111	Soguksu D	Yeşildağ	504
16-112	Akgöl	Göl Gözlem	817
16-114	Topkaya Göleti	Giriş (Saci Kara)	818
16-115	Çarşamba S.	Sorkun	505
16-117	Seyithasan D.	Seyit Hasan	506
16-120	Suğla Gölü	Göl Gözlem	818
16-123	Çığlı Reg.	Nafia Kn.	818
16-126	Ana Tah. Kan.	Gölyazı	507
16-134	Koca D.	Derebucak	508
16-135	Tekke D.	Mahmuthisar	509
16-136	Eldeş D.	Eldeş	510
16-137	Bulcuk D.	Bulcuk	511
16-138	Seki D.	Derebucak	512
16-139	Fındıklı D.	Altınapa Giriş	513
16-140	İvriz Ç.	Aydınkent	514
16-141	Zanapa D.	Halkapınar	515
16-142	İvriz Brj.	Göl Gözlem	818
16-143	İvriz Brj.	Çıkış (Ana yatak)	818
16-144	İvriz Brj. Cıkıs	Sol Ana Kn.	818
16-145	İvriz Brj. Çıkış	Sağ Ana Kn.	818
16-148	Ören D.	Gümüşler	516
16-149	Bolasan Deriv.Kan.	Saraycık	517
16-151	Çebişçi S.	Argıthan	518
16-153	Gödet barajı	Göl Gözlem	818
16-154	Ozan D.	Tolca	519
16-155	Çavuşköy D	Kıreli	520
16-157	Tuz G.	Göl Gözl.(Yavşan Tuzlası)	818
16-158	Hizar D	Gölyaka	521
16-161	Akçardak D.	Melikli	522
16-162	Zanapa D.	Dedeli	818
16-163	Anaboşaltım Kan.	Tatlıkuyu	523
16-164	T3 Tahliye Kan.	Adabağ	818
16-166	Çarşamba S.	Pınarcık	524

İst.No.	Suyun Adı	İstasyonun Adı	Sayfa
16-168	Bıçakçı D.	Sadıklar	525
16-169	Beyşehir G.	Göl Gözlem	818
16-172	Darı D.	Oğlakçı	526

17.DOĞU AKDENİZ HAVZASI

17-6	Deliçay	Puğkaraağaç	527
17-7	Pamuk D.	Keşbükü	528
17-11	Eferenk D.	Hamzabeyli	529
17-12	Lamas Ç.	Sarıaydın	530
17-14	Göksu N.	Görmel Köp.	531
17-16	Göksu N.	Kravga Köp.	532
17-17	Göksu N.	Gödröp Köp.	533
17-24	Korucak D.	Çataldeğirmen	534
17-27	Bıçkıcı D.	İnceğiz	535
17-33	Göksu	Aladağ Köp.	536
17-34	Boğaz D.	Sazak Köp.	537
17-35	Ilıcapınar D.	Korucu Köp.	538
17-37	Kaplancı D.	Dağlıkköy	539
17-38	Sedre Ç.	Kocaoğlanlı	540
17-39	Gökçeler D.	Gazipaşa	541
17-40	Alata Ç.	Sarılar	542
17-41	Bozyazı D.	Karaisalı	543
17-43	Gülek D.	Çamalan	819
17-44	Soğuksu	Aydıncık	819
17-45	Erçel D.	Değirmençayır	544
17-46	Sorgun Ç.	B.Sorgun	545
17-47	Aksıfat D.	Aksıfat Brj.	546
17-49	Lamas Ç.	Limonlu	547
17-50	Lamas Ç.	Yeniyurt	548
17-51	Pirinç S.	Gençali	549
17-52	Pamukkale Ç.	Çamlıyayla	819
17-53	Göksu N.	Kargıcık	550
17-54	Cehennem D.	Sebil	551

18. SEYHAN HAVZASI

18-1	Seyhan N	Eyner	553
18-6	Çakıt S.	Şekerpınar	554
18-8	Tacın S.	Tacın	555
18-12	Körkün S.	Kamışlı	556
18-15	Seyhan B.	Göl Gözlem	787
18-17	Sarız S.	Darıdere	557
18-18	İnderesi	Hasançavuş	558
18-19	Asmaca S.	Feke	559
18-21	Kapuz D.	Kapuz	560
18-22	Aksu Ç.	B.Sofulu	561
18-23	Yağdeğleme D.	Yeniköy	562
18-27	Ecemiş Ç.	Elekgölü	563
18-28	Ecemiş Ç.	Çukurbey	564
18-30	Zamantı N.	Mustafa Oruç	819
18-31	Zamantı N.	Göktaş	819
18-32	Sarız D.	Şarköy	565
18-34	Deliçay	Hocaali	566
18-36	Göksu N.	Feke	567
18-40	Çörümşek D.	Panlı	568
18-42	Hacıbillik Çeşmesi	Çerkezsöğüt	569
18-45	Seyhan N.	Reg.	819
18-46	Özdere	Gölet Girişi	819
18-47	Zamantı N.	Çamlıca HES	570

İst.No.	Suyun Adı	İstasyonun Adı	Sayfa
18-48	Totari D.	Bademdere	571
18-49	Eğnelliözü D.	Eğnelli	572
18-50	Hamaca D.	Bademdere	573
18-51	Eğri Ç.	B. Sofulu	574
18-52	Bahçeli Brj.	Göl Gözlem	819

19.ASİ HAVZASI

19-6	Afrin S.	Afrin Köp.	575
19-8	Emen Ana Tah. Kan.	Örtülü	576
19-9	Asi N.	Çögürlü	577
19-12	Karasu	Çolaklar	578
19-14	Deliçay	Mutlu Çukur	579
19-16	Gönen Ç.	Adamahallesi	580
19-18	Derebahçe D.	Müftü köp.	581
19-19	Sabun S.	Güneşli	582
19-20	Hüyük D.	Hüyük	583
19-21	Avcılar S.	Avcılar	584
19-22	Beyköy D.	Beyköy	585
19-23	H.Ahmet D.	H.Ahmet	586
19-26	K.Asi N.	Hasanlı köp.	587
19-27	Karasu N.	Arpahan	588
19-28	Beyazçay	Alakent	589
19-29	B.Karaçay	Yaylıca	590
19-30	Asi N.	Eşrefiye	591
19-31	Karasu N.	Kaletepe	592

20.CEYHAN HAVZASI

20-2	Aksu Ç.	Başpınar	593
20-5	Yarpuz Ç.	Çona	594
20-6	Sabun S.	Haruniye	595
20-7	Hurman S.	Kuş Kayası	819
20-8	Karaçay	Osmaniye	596
20-10	Humus S.	Arıklıkaş	597
20-13	Andıran S.	Tokmaklı	820
20-16	Kömür S.	Alıçlıbucak	820
20-17	Aksu Çayı	Köprüağzı	820
20-24	Ceyhan N.	Hamite Köp.	598
20-27	Karasu D.	İnekli Gölü Çıkışı	599
20-28	İnekli Gölü	Göl Gözlem	820
20-29	Azaklı Gölü	Göl Gözlem	820
20-30	Gölbaşı Gölü	Göl Gözlem	820
20-31	Gölbaşı Gölü	Çıkış	820
20-33	Sabun S.	Boyalı	600
20-36	Körsulu D.	Sisne	820
20-40	İceri S.	Ballıkaya	601
20-43	Kesik S.	Taşköprü	602
20-44	Dalacak D.	Dağılcak	603
20-45	Kırksu	Eskimontaj Köp.	820
20-46	Kesiş S.	Sarıdanışmanlı	604
20-47	Aksu Ç.	Hacı Must. Çift.	820
20-48	Gavur G.	Sifon Ç.	605
20-49	Erkenez Ç.	Bulanık	820
20-51	Nergele Ç.	Topalyusuflar	606
20-52	Fındık D.	Fındık	821
20-53	Fırnıs S.	Kabaktepe	607
20-54	Tekir D.	Alikesen	608
20-55	Zeytin D.	Süleymanlı	821
20-56	Bertiz Ç.	Himmetli	609

İst.No.	Suyun Adı	İstasyonun Adı	Sayfa
20-57	Çemrengeç S.	Kozcağız	610
20-58	Tahta S.	Canbazoğlu	611
20-59	Kesis D.	Keleşli	612
20-60	Kısık D.	Kısık	821
20-61	İmalı Ç.	Türkoğlu	821
20-62	Deliçay	Jandarmalar Obası	613
20-63	Orcan Ç.	Jandarmalar	614
20-64	Mizmilli Ç.	Bertizler Obası	821
20-65	Çepele D.	İmamoğlu	615
20-66	Söğüt Ç.	Karahasanuşağı	821
20-67	Hasanali D	Hasanali K.	821
20-68	Köprüağzı D.	Geben	616
20-69	Karapınar D	Geben	617
20-70	Bağlama D.	Bertizler	821
20-71	Karapınar	Kızıllar K.	618
20-72	Meletmez D.	Acarmentaş	619
20-73	Hasanbeyli D.	Hasanbeyli	620
20-74	Tekir D.	Alişar	821

21. FIRAT HAVZASI

21-1	Kara S.	Kırkgöze	621
21-4	Murat N.	Diyadin	821
21-26	Keysun Ç.	Körpınar	822
21-40	Akpınar D.	Girlevik HES	622
21-41	Peri S.	Selenk Köp.	822
21-52	Serçeme S.	Eğerli	822
21-67	Senpas S.	Kap Değirmeni	822
21-81	Balık S.	Yağızköy Köp.	623
21-85	Liz D.	Camili	822
21-87	Karahalit D.	Yeniköy	822
21-96	Sultan S.	Hara	822
21-111	Tüzel S.	Ekinci Köp.	822
21-121	Mamikan D.	Kapıkaya	624
21-127	Hazar Gölü	Göl Gözlem	822
21-132	Pulur S.	Sakalıkesik	822
21-133	Sofraz Ç.	Alişar	823
21-134	Tohma S.	Çatalbahçe	625
21-140	Cip D.	Cip Brj.Giriş	626
21-141	Mandalık S.	Yapılıköy	627
21-146	Gulap D.	Akçakale	823
21-148	Haftrenk S.	Aktuzla	628
21-149	Murat N.	Köprüköy	823
21-152	Köşk D.	Köşk	629
21-157	Şeyhan Ç.	Betonköprü	630
21-159	Kuru Ç.	Kesikköprü	631
21-160	Gülbahar D.	Hacıçayırı	632
21-162	Ayvalı Tohma S.	Göynük	633
21-166	Hınıs S.	Hınıs	634
21-167	Kisre Ç.	Necmettinağa K.	635
21-168	Büyük Ç.	Karagöbek	636
21-169	Ahırçimen Ç.	Halilçavuş	637
21-172	Eskikahta Ç.	Damlacık Köp.	823
21-173	Murat N.	Tazekent	823
21-174	Cuma Ç.	Aşağıkent	638
21-178	Cendere Ç.	Cendere Köp.	823
21-179	Caru D.	Hamzabey	639
21-180	Keydan Ç.	Behramaz	823
21-181	Keklik D.	Aş.Yenice	640
21-182	Badisan D.	Değirmendüzü	823
21-183	Akdere Ç.	Aş. Çöplü Köyü	823
21-184	Kahta Brj.	Aksyeri	824

İst.No.	Suyun Adı	İstasyonun Adı	Sayfa
21-185	Sakaltutan S.	Erkenek	824
21-186	Göksu N.	Savran	824
21-187	Ardıl Ç.	Ardıl	641
21-188	Halya D.	Genik Köp.	824
21-189	Ziyaret Ç.	Payamlı Köp.	642
21-190	Şepker Ç.	Şerefli	824
21-191	Göksu Ç.	Ozan	824
21-193	Kozluk Ç.	Asağışıhlar	643
21-194	Perisuyu	Kızılçubuk	644
21-197	Üzümlü D.	Üzümlü	824
21-198	Mercan D	Günbağı	824
21-200	Karasu	Ilıca	824
21-201	Şeriyan Ç.	Karabacak	825
21-202	Derecek D.	Derecek	825
21-203	Hınıs Ç.	Karaçoban	645
21-204	Toprakkale D.	Kavak	646
21-206	Alleben D.	Etbalık	825
21-207	Çakal D.	Kındırali	825
21-208	Eğriçay	Kırkgöz	825
21-209	Trasa Ç.	Çatalağaç	647
21-210	Büyükçay	Taşkale	648
21-211	Sincik D.	Sırımtaş	825
21-212	Handeresi	Balyanköyü	649
21-213	Adaderesi	Ağaçlı	650
21-214	Otlukbeli Ç.	Söğütlü	825
21-215	Güzeldere	Güneykaya	825
21-216	Hanoba Ç.	Dönerdere	651
21-217	Mardikdere	Çökelge	825
21-218	Cumaçay	Kayacık	825
21-219	Seyithasanbey	Seyithasanbey	826
21-220	Solandere	Göksu	652
21-222	Hamurpet Gölü	Göl Gözlem	826
21-225	Yayladere	Camlıyayla	826
21-226	Tuzla Ç.	Gökçeşeyh	653
21-227	Fırat N.	Gürlevik	826
21-230	Çatakdere	Çataksu	654
21-231	Badişandere	Karakaya	655
21-232	Kalecikdere	Dereyurt	826
21-233	Bahçeli D.	Bahçeköy	826
21-236	Otlukbeli Ç.	Çavuşkomu	826
21-237	Balıklıdere	Balıklı	826
21-238	Yazıcısuyu	Soğanlı	656
21-239	Gülkan D.	Aynalı Göleti	657
21-240	Haringet Ç.	Dedepınar	658
21-243	Bektaş D.	Akçakale	659
21-250	Çamçay	Özenpınar	660
21-251	Hamdun Ç.	Kayabaş	826
21-252	Balıklı Ç.	Esendoruk	661
21-257	Vahkın Ç	Vahkin	662
21-261	Aladağ D.	Gültepe	826
21-262	Göksu D.	Düzbağ	663
21-263	Aliağa D.	Görgüçler	664
21-264	Cevizli D.	Cevizli	665
21-265	Kırkpınar D.	Aşağimülk	666
21-266	Karadoğu D.	Beklamaz	667
21-267	Şehitler D	Baldere köyü	827
21-268	Diltop D	Atabindi	827
21-269	Nadirşeyh S.	Atabindi	668
21-270	Gülçatı D.	Gülçat	669
21-271	Şekerpınar D.	Çamurlu	670
21-272	Sürgü Ç.	Reşadiye	827
21-275	Sürgü Ç.	Pütürge	671
21-277	Yılanlı Ç.	İkizdere	672

İst.No.	Suyun Adı	İstasyonun Adı	Sayfa
21-279	Karanlık D.	Davulbaz	673
21-281	Genşugul D.	Yeniköy	674
21-282	Kazıklısuyu	Saraç	675
21-284	Kızıl D.	Karaçay	827
21-285	Avzal D.	Deregezer	827
21-286	Sığdın D.	A. Kuşağı	827
21-287	Kamışlı D.	Tatar	676
21-288	Karadere	Karadere	827
21-290	Şorak D.	Kuşçuköy	677
21-292	Han Deresi	Çiftlik	678
21-293	Güvercin D.	Mustafabey	828
21-294	Kale D.	Bakımevi	679
21-295	Balıkkaya D.	Yaylacık	828
21-297	Yağlıdere	Arıbahçe	680
21-298	Kayalar D.	Aktoprak	681
21-299	Kale D	Kale	828
21-300	Kilise D	Sancak	682
21-301	Lavaşan D.	Karlıova	828
21-302	Kale D.	Yarmak	828
21-304	Söğütlü D.	Deregezen	683
21-305	Mahmudiye D.	Çamurlu	684
21-306	Midye Ç.	Oyuklu köyü	685
21-307	Gökçe D.	Gökçe	686
21-308	Aksu Ç.	Dereköy	828
21-309	Karakoyun D.	Direkli	828
21-310	Tohma S.	Gürün	687

26. DİCLE HAVZASI(21 NOLU FIRAT HAVZASI İLE BİRLEŞMİŞTİR)

26-8	Pamukluk D.	Dilaver Köp.	688
26-12	Başnik Ç.	Salat	689
26-16	Dankıran	Selimi	690
26-30	Zap S.	Çaldıran Köp.	829
26-32	Pamuk Ç.	Karahan Köp.	691
26-33	Çatak S.	Çatak	829
26-34	Zap S.	Debin Köp.	829
26-36	Zap S.	Üzümcü	829
26-37	Zap S.	Geyman	829
26-39	Ambar Ç.	Hani	692
26-40	Mehmediyan Ç.	Tepecik	693
26-43	Nahil Ç.	Konaklı Köp.	829
26-44	Büyük Ç.	Mezreköy	829
26-47	Uludere	Kadınlık	829
26-48	Hezil S.	Şenoba	829
26-51	Müküs Ç.	Bahçesaray	829
26-52	Kulp Ç.	Kulp Köp.	829
26-54	Kızılsu	Kasrik	694
26-55	Çatak D.	Dalbastı	695
26-56	Büyük Ç.	Dilimli	830
26-57	Keyburan S.	Boğazönü	830
26-60	Başkoy Ç.	Kıbrıs	696
26-62	Sallar Ç.	Yolköprü	697
26-63	Kodi D.	Kodeköy (2005)	698-699
26-64	Çelikdere	Güçlüköy	700
26-65	Esen D.	Esendere	830
26-66	Şemdinli S.	Navroz Köprüsü	830
26-67	Dicle N.	Cizre	830

22.DOĞUKARADENİZ HAVZASI

22-6	Abuçağlayan D.	Köprübaşı	701

İst.No.	Suyun Adı	İstasyonun Adı	Sayfa
22-7	Haldizen S.	Şerah	702
22-9	Harşit Ç.	Torul	703
22-13	Kavraz D.	Süttaşı	704
22-40	Harşit Ç.	Eymür	705
22-44	Karadere	Aytaş	706
22-48	Uzungöl	Göl Gözlem	830
22-49	Kapistra D.	Başköy	707
22-52	Solaklı D.	Ulucami	708
22-53	Sürmene D.	Ortaköy	709
22-55	Melet Ir.	Yeşilyurt	830
22-56	Turna S.	Turnaköy	830
22-57	Ögene D.	Alçak Köp.	830
22-58	Görele D.	Cücen Köp.	710
22-59	Kalyon D.	Çiftdere	711
22-62	Hemşin D.	Konaklar	712
22-63	Hala D.	Mikron Köp.	713
22-64	Pazar S.	Kovanlık	714
22-67	Sap S.	Durakköy	715
22-72	Arılı D.	Arılı	831
22-73	Yağlı D.	Tuğlacık	716
22-78	Tozköy D.	Tozköy	717
22-79	Kapistra D.	Çamlıca	831
22-80	Yağlı D.	Sinirköy	718
22-81	Güney S.	Zincirli Köprü	831
22-82	Salarha D.	Kömürcüler	719
22-83	KodiliÇ.	Gümüşkaya	720
22-84	Korum D.	Yağlıdere İkisu	721
22-85	Şenöz D.	Kaptanpaşa	722
22-86	Değirmendere	Ögütlü	831
22-87	Gelevera D.	Hasanşeyh	723
22-89	Ballı D.	Küçükköy	724
22-91	Bolaman Ç.	Çatalpınar	725
22-92	Reşadiye Ç.	Kabataş	726
22-93	Turna Suyu	Cumhuriyet	727
22-95	Yayla D.	Söğütağı	728
22-96	Cimil D.	Köknar	729
22-97	Maçka D.	Osmanüstü	730
22-98	Aksu D.	Sürmen	831
22-101	Altın D.	Bakırcılar	731
22-102	Kalyan D.	Bibat	831
22-103	Değirmen D.	Sanayi Sitesi	831
22-104	Değirmen D.	Çeşmeler	831
22-105	Değirmendere	Salıpazarı	732
22-106	Batlama D.	Çukurköy	733
22-107	Söğütlü D.	Doğanköy	734
22-108	Hemşin D.	Başköy	735

23.ÇORUH HAVZASI

23-1	Berta S.	Berta	737
23-3	Çengül D.	Erikdibi	738
23-6	Pulur Ç.	Cibre	739
23-10	Çoruh N.	Şehitlik	831
23-16	Çoruh N.	Mescitli	740
23-23	Oltu Ç.	Kesikköprü Çift.	831
23-24	Oltu Ç.	Ayvalı Köy	831
23-26	Büyük Ç.	Uzunkavak	741
23-27	Masat D.	Kuşkayası	832
23-28	Büyük C.	Çatıksu	742
23-29	Haho D.	Göldere	743
23-31	Konak D.	Sırakonak	744

İst.No.	Suyun Adı	İstasyonun Adı	Sayfa
23-32	Tepe D.	Yellitepe	745
23-37	Başkale Ç.	Yanıktaş	746
23-38	Göllü D.	Yanıktaş	832
23-39	Karapınar D.	Karapınar	832
23-40	Tortum Ç	Dikyar	832
23-41	Esendurak Ç.	Tortumkale	747
23-42	Göktepe	Kaleboynu	748

24. ARAS HAVZASI

24-9	Karahan S.	Akyaka	749
24-10	Kars Ç.	Şahnalar	750
24-18	Kantarlı Ç.	Çayağzı	751
24-20	Aras N.	Sürmeli	752
24-22	Güney D.	Tansuk	832
24-28	Kekeç S.	Eskigeçit	832
24-29	Aras N.	Karakurt	753
24-32	Balık Gölü	Göl Çıkışı	832
24-33	Balık Gölü	Göl Gözlem	832
24-38	Nalbant D.	Yastıktepe	832
24-40	Masat D.	Bulkasım	754
24-41	Acıçay	Kandilli	832
24-42	Hasankale Ç.	Eğirmez	832
24-44	Abbasgöl D.	Abbasgöl	833
24-45	Taşlıdere	Abbasgöl	833
24-46	Madrak S.	Hasan Aga K.	755
24-48	Digor S.	Gülhayran	756
24-49	Digor S.	Hisarönü	757
24-50	Kayınlık D.	Balçeşme	758
24-52	Sarısu	Topçatan	833
24-53	Kura N.	Çatalköprü	759
24-58	Kışla D.	Çayırdüzü	760
24-59	Çıldır Gölü	Göl Gözlem	833
24-60	Köyaltı D.	Çatalören	761
24-63	Cot Suyu	Koyunpınar	762
24-64	Hercikli D.	Varlı	833
24-65	Türkmen D.	Senemoğlu	833
24-66	Aras N.	Halimcan	763
24-67	Balık Gölü S.	Tanıktepe	833
24-68	Kura S.	Durançam	833
24-69	Sarıkamış S.	Yağbasan	764
24-70	Susuz D.	Susuz	833
24-71	Büyükdere	Büyükdere	765
24-73	Katranlı S.	Bölükbaş	766
24-74	Çubukdere	Çatak (2003-2005)	767-768
24-78	Acıçay	Hamurkesen	833
24-79	Sarısu	Gülveren	769
24-80	Posof Ç.	Posof	770
24-81	Çamlıkale D	Dönertaş	771
24-83	Süngütaş D	Çermik	772
24-84	Yarbogaz D	Yarboğaz	773
24-85	Karayazı D	Karasuköyü	774
24-86	Hanak Ç	Hanak	834
24-87	Değirmen D	Kağızman	834
24-88	Kars Ç.	Alabalık R.	834
24-89	Digor S.	Düzgeçit	775
24-90	Karahan Ç.	Taşdere	776
24-91	Kars Ç.	Fakülte Önü	777
24-92	Soğuksu	Karataş	778
24-93	Göktaş D.	Kağın	834
24-94	Alabalık D.	Koçköyü	779
24-95	Kötek Ç.	Kötek	834

25. VAN GÖLÜ HAVZASI

25-13	Deliçay	Payköy	781
25-21	Gevaş S.	Gevaş	834
25-24	Bendimahi Ç.	Muradiye (Gönderme)	834
25-25	Memedik S.	Tepedam	834
25-31	Çubuklu S.	Çubuklu	834
25-32	Yoğurtyemez S.	Kınalıkoç	834
25-36	Van G.	Göl Gözlem (Gevaş)	835
25-37	Özalp	Kapıköy	835
25-38	Güzelkonak	Gevaş	835
25-39	Gevaş	Güzelkonak	835
25-40	Kotum Ç.	Tatvan	835

KİTABIN İÇERİĞİ, AÇIKLANMASI VE DÜZENLENİŞ YÖNTEMLERİ

DSİ Genel Müdürlüğü'nce işletilmekte olan 1189 adet Akım ve Göl Gözlem istasyonuna ilişkin veriler, DSİ Bölge Etüd ve Plan Şube Müdürlükleri Rasatlar Baş Mühendisliklerince ve Rasatlar Şube Müdürlüğü'nce 'Su Veri Tabanı Rasatlar Modülü' yazılımı kullanılarak değerlendirilmiş; '2006 AKIM GÖZLEM YILLIĞI' adıyla yayınlanmıştır.

EİE Genel Müdürlüğünce çalıştırılmakta olan Akım ve Göl Gözlem İstasyonlarını kapsayan veriler de adı geçen kurumca 'AKIM NETİCELERİ' adlı kitaplarda her su yılı için yayınlanmaktadır.

2006 AKIM GÖZLEM YILLIĞI ÜÇ BÖLÜM OLARAK DÜZENLENMİŞTİR

1.Bölümde; 01.10.2005 - 30.09.2006 tarihleri arasında açık durumda bulunan ve değerlendirilen 766 adet AGİ ile çeşitli sorunlar nedeniyle sonradan değerlendirilen ya da yeniden değerlendirilen ve bu su yılı kitabında yayınlanan 5 adet AGİ verileri yer almaktadır.

2.Bölümde; 01.10.2005 - 30.09.2006 tarihleri arasında açık durumda bulunan ve değerlendirilen 5 adet GGİ verileri yer almaktadır.

3.Bölümde; 01.10.2005 - 30.09.2006 tarihleri arasında açık durumda bulunan, ancak hidrometrik değerlendirme standartlarını karşılayamadığı için değerlendirilemeyen 413 adet Akım ve Göl Gözlem istasyonuna ait bilgiler yer almaktadır.

1.BÖLÜMLE İLGİLİ AÇIKLAMALAR

1.1 ORTALAMA AKIMLAR (m^3/s) :

Gözlem süresinde ortalama akım: İstasyonun açıldığı tarihten başlayarak 30.09.2005 gününe kadar değerlendiği süre içinde, günlük ortalama akımların ortalamasıdır.

2006 su yılında ortalama akım: 01.10.2005 – 30.09.2006 tarihleri arasında hesaplanan günlük ortalama akımların ortalamasıdır.

1.2 EN ÇOK VE EN AZ AKIMLAR (m^3/s) :

Gözlem süresinde anlık en çok ve en az akım: İstasyonun açıldığı tarihten başlayarak 30.09.2006 gününe kadar değerlendiği süre içinde seviye ölçerlerce saptanan seviyelerin en büyüğünün ve en küçüğünün karşıtı bulunan anlık akımlardır.

2006 su yılında anlık en çok ve en az akım: 01.10.2005 – 30.09.2006 tarihleri arasında seviye ölçerlerince saptanan seviyelerin en büyüğünün ve en küçüğünün karşıtı bulunan anlık akımlardır.

1.3 2005 SU YILINDA GÜNLÜK AKIMLAR (m^3/s) :

01.10.2005 –30.09.2006 tarihleri arasında AGİ'lerin günlük orta seviyelerinin karşıtı olan akımlardır.

1.4 AYLIK TOPLAM AKIM (hm^3/s) :

Kapsadığı ay içinde ait olduğu istasyon kesitinden geçen toplam suyun milyon metreküp veya hektometreküp cinsinden hacmidir.

1 .5 AYLIK EN ÇOK VE EN AZ AKIMLAR (m^3/s) :

Kapsadığı ay içindeki günlük seviyelerin en büyüğü ve en küçüğünün karşıtı olan anlık akımlardır.

1.6 AYLIK ORTALAMA AKIM (m^3/s) :

Kapsadığı ay içinde günlük orta seviyelerinin karşıtı olan akımların ortalamasıdır.

1.7 HAVZA VERİMİ ($lt/ sn/km^2$) :

Aylık ortalama akımın bin ile çarpılıp yağış alanına bölünmesinden elde edilen değerdir. Regülatörlerde, kanallarda, baraj çıkışlarında ve göl ayaklarında mevcut istasyonların yağış alanı olmadığı için havza verimleri hesaplanmaz.

1.8 AKIŞ YÜKSEKLİĞİ (mm) :

Aylık toplam akımın bin ile çarpılıp yağış alanına bölünmesinden elde edilen mm cinsinden akış yüksekliğidir. Yağış alanı olmayan istasyonlarda akış yüksekliği hesaplanmaz.

1.9 AKIM ANAHTARLARININ BELİRLİ SEVİYELERİNİ KAPSAYAN AKIMLAR:

Su yılı içinde en uzun süre kullanılan akım anahtarının belli sayıdaki karakteristik değerleridir. AGİ'deki belirli seviyelerin karşılığı debiler veya belirli debilerin karşılığı eşel seviyeleri yaklaşık olarak bu küçük tablo yardımı ile bulunabilir.

2. BÖLÜMLE İLGİLİ AÇIKLAMALAR

2.1 EN YÜKSEK VE EN DÜŞÜK SEVİYE (cm) :

Gözlem süresinde en yüksek ve en düşük seviye: İstasyonun açıldığı tarihten 30.09.2006 tarihine kadar, seviye ölçerlerince tespit edilen en yüksek ve en düşük seviyelerdir.

2006 su yılında en yüksek ve en düşük seviye: 01.10.2005 – 30.09.2006 tarihleri arasında seviye ölçerlerince tespit edilen en yüksek ve en düşük seviyelerdir.

Su yılı içinde tam gözlem yapılamayan Göl Gözlem İstasyonlarında en düşük ve en yüksek seviyeler verilmemiştir.

2.2 GÜNLÜK SEVİYELER :

Her gün saat 8.00 de seviye ölçerlerince tespit edilen göl su seviyeleri günlük seviye olarak alınır. Önceki yıllarda H=(a+13b+4c) / 18 formülü ile bulunan orta seviyeler göllerde günlük seviye değişimlerinin büyük olmayacağı göz önüne alınarak 1979 yılında bırakılmıştır.

2.3 AYLIK EN YÜKSEK VE EN DÜŞÜK SEVİYE :

Kapsadığı ay içinde seviye ölçerlerince saptanan en yüksek ve en düşük seviyeler.

2.4 AYLIK ORTALAMA SEVİYE :

Günlük ortalama seviyelerinin toplamının, kapsadığı ayın gün sayısına bölünmesinden elde edilen seviyedir.

3. BÖLÜM

3.1 AKIM ÖLÇÜMLERİ :

01.10.2005-30.09.2006 tarihleri arasında değerlendirilemeyen AGİ'lerde yapılan akım ölçüleri: Ölçünün yapıldığı tarihler, seviyeler (cm) ve debiler (m^3/s) olarak verilmiştir. Bu akım ölçüleri akım anahtarı çizilmesi ve hidrometrik değerlendirme yapılması için yeterli görülmemiştir.

Bu gözlem yıllığında yer alan gözlem istasyonlarının koordinatları, yağış alanları ve kot (rakım) bilgileri, 1/100000 ve 1/250000 ölçekli haritalardan çıkarılmıştır.

Baraj çıkışında, göl ayağında bulunan regülatörlerde, sulama kanallarında bulunan gözlem istasyonlarında, yağış alanı ve kot bilgisi verilmemiştir.

VERİLERİN GÜVENİRLİĞİ :

Akarsu akım değerlerinin belirlenmesinde; gerek akım ölçüsünün yapılmasında ve gerekse değerlendirilmesinde bazı yanılgılar olabilir. Bunları özetlemek gerekirse;

- Yöntem yanılgısı,
- Hız ölçüm aletinden (muline) gelen yanılgılar,
- Hidroloğun kişisel yanılgıları,
- Abak hatalarından doğan yanılgılardır.
- Düşey ve yatay sapma düzeltmeleri yapılmadığı için ortaya, çıkan alan saptanmasındaki yanılgılar,
- Seviye saptama yanılgıları,
- Orta seviye hesabındaki yanılgılar,
- Akım ölçüsü hesabındaki yanılgılar,
- Akım anahtarının, yanlış çizilmesinden ya da doğru anahtarın yanlış okunmasından doğan yanılgılardır.

Bu durumlar dikkate alınarak uluslararası saptanmış sınırlara göre, akım ölçülerinin yapılış ve değerlendirilmesinde, göz önünde tutulan yanılgı sınırları;

< % 2 ise akım ölçüsü başarılı,
< % 5 ise akım ölçüsü iyi,
< % 8 ise akım ölçüsü orta,
> % 8 ise akım ölçüsü yetersizdir.

Bu yayının değerlerinde olabilecek yanılgı oranı sınırları;

< % 5 ise verilen değerler başarılı,
< %10 ise verilen değerler iyi,
< % 15 ise verilen değerler orta,
> % 15 ise verilen değerler yetersizdir.

DSİ gözlem yıllığında yayınlanan günlük akım değerlerinde % 5' e denk gelen yanılgı kabul edilmiştir.

ORTALAMA SAPMALARDA OLABİLİRLİK YANILGI FORMÜLÜ :

$$\text{Ortalamanın Olabilir Yanılgısı} = \frac{\text{Tek Tek Değerlerin Olabilir Yanılgısı}}{N^{0.5}}$$

dir.

Aylık ortalamalarda N=30 alınarak; aylık ortalamaların olabilir yanılgısının, günlük ortalamaların olabilir yanılgısının bu formüle göre yaklaşık olarak 1:5'i olacağı görülür. Bu nedenle aylık ortalamalar üç basamaklı olarak verilmesi halinde içine düşülen yanılgı % 14'ün altındadır.

Zira :

5/100*1/5 = 5/500 = 0.01 < 0.14 dür.

Yıllık ortalamalarda ise, aynı formülden yıllık ortalamanın olabilir yanılgısının günlük ortalamaların olabilir yanılgısının yaklaşık olarak 1/20'si olacağı görülür. Bu nedenle yıllık ortalamalar ondalıklı sayıların üç basamaklı olarak verilmesi halinde içine düşülen yanılgı oranı formülden bulunan %0.25'inin en çok 1:4'ü olmaktadır.

İlk defa 1989 su yılında uygulanmasına başlanan sistemle; DSİ Bölge Müdürlükleri Rasatlar Baş Mühendisliği personelince AGİ'lere ve GGİ'lere ait tüm veriler, Genel Müdürlüğümüz Rasatlar Şube Müdürlüğü'ne "Hidro" yazılımı verisi olarak elektronik ortamda aktarılmış, hidrometrik değerlendirmeler yine "Hidro" yazılımı kullanılarak yapılmıştır.

2006 Akım Yıllığı kitap sayfalarının hazırlanması ise, Rasatlar Şube Müdürlüğü 'Hidrometri Değerlendirme Merkezi'nce "Su Veri Tabanı Rasatlar Modülü" yazılımı kullanılarak tamamlanmıştır.

Kitap, DSİ Matbaası tarafından basılmış ve çoğaltılmıştır.

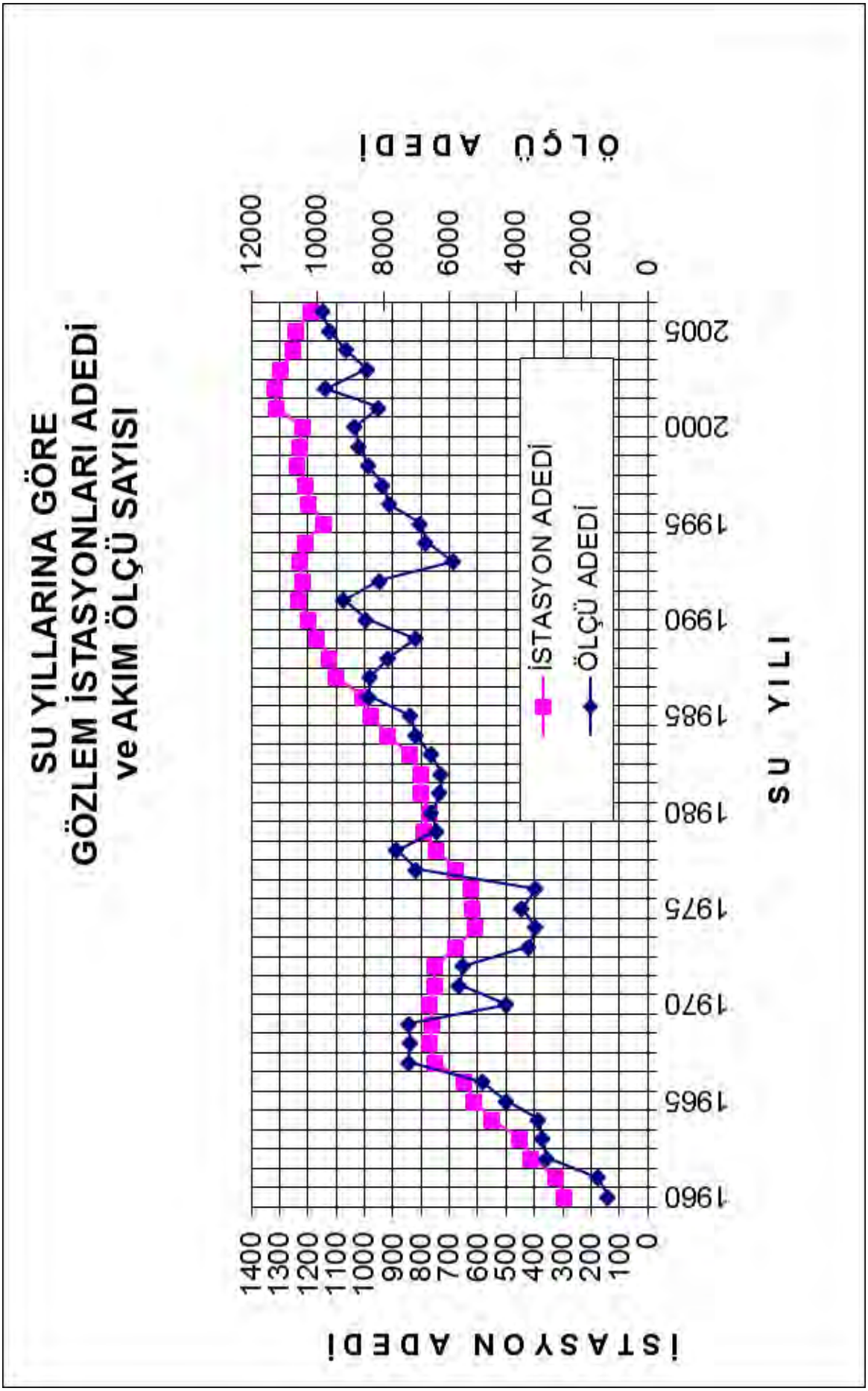
SU YILLARINA GÖRE
GÖZLEM İSTASYONLARI ADEDİ
ve AKIM ÖLÇÜ SAYISI
İSTASYON ADEDİ
ÖLÇÜ ADEDİ
SU YILI
İSTASYON ADEDİ
ÖLÇÜ ADEDİ
1400
1300
1200
1100
1000
900
800
700
600
500
400
300
200
100
0
12000
10000
8000
6000
4000
2000
0
1960
1965
1970
1975
1980
1985
1990
1995
2000
2005

BÖLÜM I

AKIM ANAHTARI MEVCUT İSTASYONLARIN AKIM DEĞERLERİ

01
MERİÇ HAVZASI

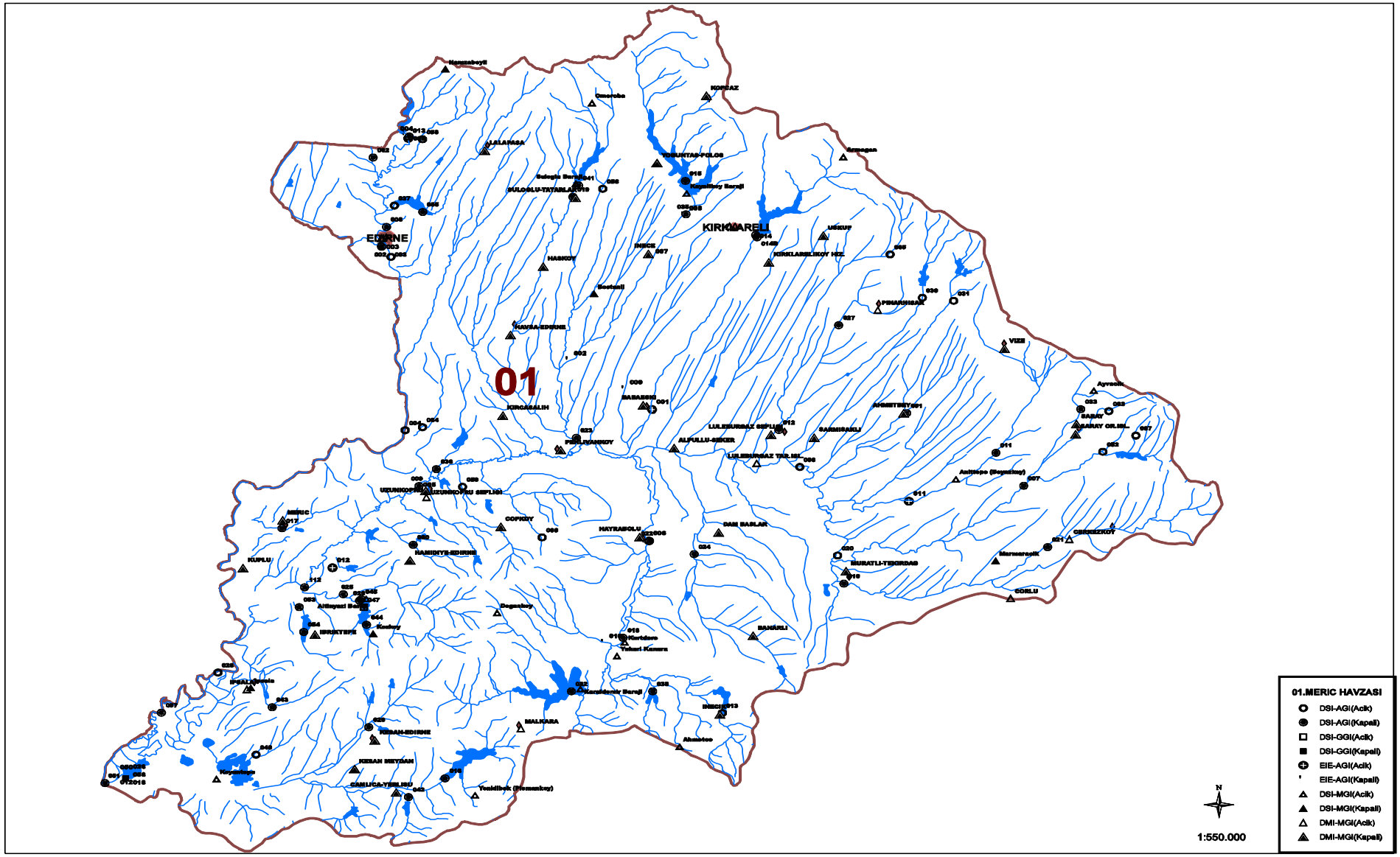
01
EDIRNE
KIRKLARELI
01.MERIC HAVZASI
DSI-AGI(Acik)
DSI-AGI(Kapali)
DSI-GGI(Acik)
DSI-GGI(Kapali)
EIE-AGI(Acik)
EIE-AGI(Kapali)
DSI-MGI(Acik)
DSI-MGI(Kapali)
DMI-MGI(Acik)
DMI-MGI(Kapali)
N
1:550.000

01. Meriç-Ergene Havzasi

D01A003 MERİÇ N. KİRİŞHANE

YERİ : MERIC NEHRI ILE TUNCA NEHIRLERININ BIRLESIMINDEN YAKLASIK 300 M MANSAPTA. E17D1
26°34'20" Doğu - 41°38'50" Kuzey

YAĞIŞ ALANI : 34990,00 km2 YAKLAŞIK KOT : 31 m

GÖZLEM SÜRESİ : 30.05.1985 - 30.09.2006

ORTALAMA AKIMLAR : Gözlem süresinde 135.196 m3/sn. (21 Yıllık) 2006 Su yılında 295.110 m3/sn.

ANLIK EN ÇOK VE EN AZ AKIMLAR:

2006 Su yılında anlık ençok akım	:	1791	m3/sn	14.03.2006
2006 Su yılında anlık enaz akım	:	77.0	m3/sn	18.08.2006
Gözlem süresinde anlık ençok akım	:	2200	m3/sn	04.03.1965
Gözlem süresinde anlık enaz akım	:	0.450	m3/sn	25.07.1990

7. Anahtar Eğrisi (Seviyeler cm olarak)

Seviye	Akım	Seviye	Akım	Seviye	Akım	Seviye	Akım
2	1.7	43	51.2	60	77.0	321	797.
10	9.6	44	52.6	80	108.	452	1290.
20	20.5	45	54.0	132	219.	500	1552.
30	33.0	46	55.4	200	401.	600	2149.
40	47.0	50	61.0	298	707.	800	3200.

Akımlar 01 Ekim 2005 'den 30 Eylül 2006' a kadar m3/sn olarak

Gün	Ekim	Kasım	Aralık	Ocak	Şubat	Mart	Nisan	Mayıs	Haziran	Temmuz	Ağustos	Eylül
01	169.	192.	303.	566.	199.	791.	605.	331.	169.	167.	92.5	142.
02	187.	141.	217.	650.	254.	847.	538.	314.	134.	151.	100.	122.
03	176.	139.	254.	701.	242.	853.	526.	318.	134.	153.	102.	114.
04	259.	147.	272.	708.	264.	810.	599.	290.	126.	309.	153.	116.
05	355.	147.	256.	669.	242.	620.	568.	276.	122.	374.	106.	126.
06	334.	145.	294.	685.	228.	553.	514.	270.	122.	254.	116.	112.
07	285.	139.	288.	794.	264.	526.	404.	242.	140.	226.	97.2	106.
08	294.	143.	208.	919.	235.	593.	446.	230.	132.	252.	89.4	106.
09	217.	136.	217.	887.	239.	676.	547.	228.	153.	195.	94.1	106.
10	223.	139.	205.	724.	235.	695.	584.	224.	165.	169.	100.	98.7
11	280.	147.	228.	641.	196.	685.	562.	207.	163.	173.	106.	97.2
12	196.	130.	212.	629.	214.	743.	584.	213.	179.	159.	105.	100.
13	196.	130.	226.	514.	214.	1052	590.	211.	197.	167.	100.	112.
14	185.	160.	205.	520.	223.	1690	511.	209.	218.	140.	97.2	114.
15	187.	167.	288.	487.	247.	1551	526.	207.	199.	149.	87.9	114.
16	165.	141.	283.	420.	205.	1249	488.	203.	197.	163.	92.5	108.
17	171.	162.	239.	398.	208.	1181	508.	201.	189.	199.	83.2	108.
18	153.	109.	226.	377.	180.	1060	491.	191.	191.	211.	80.1	102.
19	153.	136.	217.	361.	196.	946.	471.	193.	193.	177.	83.2	100.
20	153.	167.	280.	355.	237.	895.	532.	185.	175.	169.	83.2	110.
21	174.	155.	291.	368.	247.	804.	526.	179.	177.	189.	86.3	105.
22	180.	149.	311.	364.	226.	679.	474.	177.	169.	161.	86.3	175.
23	143.	194.	343.	314.	285.	714.	424.	189.	185.	124.	97.2	130.
24	136.	214.	303.	383.	280.	688.	393.	199.	155.	105.	108.	105.
25	128.	210.	266.	323.	408.	620.	421.	173.	145.	95.6	102.	100.
26	123.	417.	239.	326.	556.	626.	421.	185.	147.	102.	100.	169.
27	139.	383.	297.	386.	740.	626.	385.	163.	149.	98.7	102.	179.
28	171.	380.	380.	349.	788.	587.	360.	167.	173.	105.	100.	183.
29	174.	343.	475.	237.	-----	544.	435.	155.	197.	97.2	112.	207.
30	187.	266.	532.	244.	-----	565.	388.	151.	159.	98.7	120.	218.
31	156.	-----	553.	205.	-----	581.	-----	138.	-----	95.6	134.	-----
Maks.	389.	478.	584.	957.	794.	1791	656.	358.	261.	438.	211.	272.
Min.	120.	109.	189.	201.	178.	438.	338.	134.	118.	89.4	77.0	95.6
Ortalama	195.	188.	287.	500.	288.	808.	494.	214.	165.	169.	101.	126.
LT/SN/Km2	5.58	5.36	8.21	14.3	8.22	23.1	14.1	6.10	4.72	4.82	2.87	3.61
AKIM mm.	14.9	13.9	22.0	38.3	19.9	61.9	36.6	16.3	12.2	12.9	7.70	9.35
MİL. M3	523.	486.	770.	1340	696.	2164	1281	572.	428.	452.	269.	327.

SU YILI (2006) YILLIK TOPLAM AKIM 9308.00 MİLYON M3 266 MM. 8.4 LT/SN/Km2

01. Meriç-Ergene Havzasi

D01A008 ERGENE N. LULEBURGAZ

YERİ : DDY KOPRUSUNUN 50 M MENBA'INDA-SAG SAHILDE-F18B4
27°21'6" Doğu - 41°21'3" Kuzey

YAĞIŞ ALANI : 2794,00 km2 **YAKLAŞIK KOT :** 38 m

GÖZLEM SÜRESİ : 03.06.1948 - 30.09.2006

ORTALAMA AKIMLAR : Gözlem süresinde 8.324 m3/sn. (46 Yıllık) 2006 Su yılında 9.266 m3/sn.

ANLIK EN ÇOK VE EN AZ AKIMLAR:

2006 Su yılında anlık ençok akım	:	99.6	m3/sn	12.06.2006
2006 Su yılında anlık enaz akım	:	4.42	m3/sn	07.11.2005
Gözlem süresinde anlık ençok akım	:	1100	m3/sn	26.10.1975
Gözlem süresinde anlık enaz akım	:	0.000	m3/sn	02.08.1961

9. Anahtar Eğrisi (Seviyeler cm olarak)

Seviye	Akım	Seviye	Akım	Seviye	Akım	Seviye	Akım
25	0.000	56	0.730	240	10.2	500	137.
36	0.100	63	0.970	290	16.2	550	410.
41	0.250	90	2.0	350	26.0	600	885.
46	0.400	140	4.1	400	40.0		
51	0.580	190	6.8	450	65.4		

Akımlar 01 Ekim 2005 'den 30 Eylül 2006' a kadar m3/sn olarak

Gün	Ekim	Kasım	Aralık	Ocak	Şubat	Mart	Nisan	Mayıs	Haziran	Temmuz	Ağustos	Eylül
01	5.74	5.31	6.52	7.52	7.45	46.0	8.53	6.58	6.03	6.09	5.46	5.68
02	6.03	5.36	6.40	9.98	7.77	21.3	7.71	6.40	6.03	6.15	5.74	5.74
03	6.27	5.26	6.34	8.89	8.17	21.3	7.90	6.58	5.91	17.7	5.86	5.68
04	6.09	4.71	6.58	8.25	9.33	17.0	7.71	6.65	5.97	56.0	5.86	5.31
05	5.80	4.56	6.15	7.90	10.4	11.0	7.77	6.58	5.56	29.7	5.80	5.21
06	5.86	4.51	5.74	7.65	10.4	11.0	7.90	6.58	5.41	10.8	5.74	5.56
07	5.80	4.47	5.97	7.45	10.1	33.9	7.84	6.52	5.80	8.61	5.41	5.68
08	5.80	4.81	6.09	7.20	8.61	57.2	7.84	6.21	5.97	7.71	5.21	5.68
09	5.74	5.41	6.21	6.71	7.84	21.9	7.84	6.09	6.77	7.20	5.68	5.68
10	5.51	5.74	6.27	6.15	8.32	17.3	7.58	6.65	14.6	6.65	5.80	5.62
11	5.26	5.80	6.09	5.80	9.69	28.1	7.27	6.46	68.7	6.34	5.74	5.41
12	5.62	5.80	5.80	5.62	18.7	75.6	7.45	6.96	27.2	6.65	5.74	5.16
13	5.80	5.80	5.56	5.74	26.0	47.6	7.33	6.96	9.62	6.58	5.62	5.51
14	5.74	5.62	5.86	8.25	18.7	77.5	7.33	6.83	8.61	6.52	5.31	5.68
15	5.80	5.46	6.03	10.2	14.1	59.6	7.20	6.34	7.97	6.52	5.11	5.68
16	5.74	5.80	6.15	7.77	11.0	29.5	7.14	6.09	8.61	6.65	5.46	5.68
17	5.56	5.91	6.34	7.52	9.84	18.6	6.96	6.34	8.17	6.03	5.62	5.62
18	5.31	5.91	7.33	7.90	9.40	14.0	6.83	6.46	7.33	5.74	5.62	5.41
19	5.56	6.03	11.1	7.84	19.1	11.3	6.96	6.34	6.83	6.15	5.51	5.26
20	5.68	6.40	15.8	7.90	39.6	10.2	7.08	6.34	6.52	6.15	5.31	5.62
21	5.68	6.52	12.2	16.8	29.2	9.98	7.02	5.97	6.71	6.15	5.11	6.09
22	5.74	5.80	8.82	12.6	25.8	9.62	7.02	5.68	6.71	6.09	5.46	5.97
23	5.68	5.91	7.97	9.04	19.6	9.62	7.02	5.56	6.52	6.03	5.68	6.09
24	5.51	6.46	7.27	8.61	17.9	13.3	6.71	6.09	6.65	5.68	5.68	6.09
25	5.31	7.02	6.89	7.39	16.1	13.2	6.46	6.21	6.34	5.51	5.62	5.68
26	5.56	7.65	6.46	6.65	21.2	9.91	6.65	6.21	5.97	5.91	5.62	5.97
27	5.74	7.97	6.96	6.27	39.6	8.89	6.77	6.21	5.68	5.97	5.62	6.83
28	5.74	7.02	8.97	6.83	43.6	8.97	6.77	6.15	6.03	5.97	5.31	6.21
29	5.74	6.52	8.61	7.20	-----	8.75	6.77	5.86	6.15	5.91	5.36	6.27
30	5.36	6.65	9.33	7.08	-----	8.75	6.77	5.68	6.09	5.80	5.80	6.40
31	5.36	-----	9.98	7.02	-----	8.53	-----	5.91	-----	5.31	5.68	-----
Maks.	6.46	8.25	17.7	18.9	59.6	95.2	8.75	7.08	99.6	74.7	5.91	7.39
Min.	5.21	4.42	5.51	5.56	7.27	8.25	6.46	5.56	5.31	5.31	5.06	5.16
Ortalama	5.68	5.87	7.48	7.99	17.1	23.9	7.27	6.31	9.68	9.17	5.57	5.75
LT/SN/Km2	2.03	2.10	2.68	2.86	6.10	8.54	2.60	2.26	3.47	3.28	1.99	2.06
AKIM mm.	5.45	5.45	7.17	7.66	14.8	22.9	6.75	6.05	8.98	8.79	5.34	5.33
MİL. M3	15.2	15.2	20.0	21.4	41.3	63.9	18.8	16.9	25.1	24.6	14.9	14.9

SU YILI (2006) YILLIK TOPLAM AKIM 292.20 MİLYON M3 105 MM. 3.3 LT/SN/Km2

01. Meriç-Ergene Havzasi

D01A020 ERGENE N. INANLI

YERİ : **MURATLI YA 4.5 KM MESAFEDEKI INANLI KOYUNUN 200 M. MANSABINDADIR.- F18C2**
27°28'0" Doğu - 45°78'0" Kuzey

YAĞIŞ ALANI : **1415,00 km2** **YAKLAŞIK KOT : 58 m**

GÖZLEM SÜRESİ : **22.08.1961 - 30.09.2006**

ORTALAMA AKIMLAR : **Gözlem süresinde 4.956 m3/sn. (42 Yıllık) 2006 Su yılında 7.708 m3/sn.**

ANLIK EN ÇOK VE EN AZ AKIMLAR:

2006 Su yılında anlık ençok akım	**:**	**110.**	**m3/sn**	**12.06.2006**
2006 Su yılında anlık enaz akım	**:**	**2.20**	**m3/sn**	**06.11.2005**
Gözlem süresinde anlık ençok akım	**:**	**340.**	**m3/sn**	**25.12.2001**
Gözlem süresinde anlık enaz akım	**:**	**0.000**	**m3/sn**	**01.08.1962**

İstasyon için kullanılmış anahtar bulunamadı.

Akımlar 01 Ekim 2005 'den 30 Eylül 2006' a kadar m3/sn olarak

Gün	Ekim	Kasım	Aralık	Ocak	Şubat	Mart	Nisan	Mayıs	Haziran	Temmuz	Ağustos	Eylül
01	4.33	3.65	4.98	6.85	5.45	31.8	7.90	5.65	5.65	6.68	6.23	6.50
02	4.98	3.65	4.89	7.79	5.94	23.0	7.79	5.75	5.75	6.59	5.94	6.50
03	5.45	3.26	5.26	7.68	6.23	21.9	7.56	5.84	5.84	6.68	6.32	6.50
04	4.42	2.76	5.36	6.04	7.12	14.1	7.03	6.23	5.75	12.5	6.50	6.41
05	4.52	2.58	4.33	5.84	9.39	16.2	6.76	6.32	5.65	34.4	6.59	6.04
06	4.42	2.40	4.04	5.55	9.80	10.9	7.03	6.23	5.17	11.5	6.59	5.75
07	4.42	2.40	4.42	5.26	9.59	9.00	7.03	6.13	4.89	9.09	6.50	6.23
08	4.33	2.76	4.61	4.98	8.12	9.00	6.94	6.13	5.55	8.42	6.13	6.41
09	4.33	3.55	4.70	4.61	6.94	30.7	7.12	5.65	5.75	8.12	5.75	6.50
10	3.85	4.04	4.61	4.23	6.59	23.0	7.12	5.65	6.32	7.68	6.41	6.50
11	3.55	4.33	4.42	3.75	7.79	13.9	6.59	6.23	43.9	6.94	6.59	6.50
12	4.23	4.42	4.04	3.26	12.2	12.5	6.41	6.23	32.7	6.68	6.59	6.23
13	4.33	4.33	3.75	3.16	23.5	25.6	6.76	6.50	9.80	6.94	6.59	5.65
14	4.33	4.04	4.42	4.42	19.1	27.5	6.85	6.76	8.52	7.03	6.59	6.13
15	4.33	3.94	4.52	10.6	13.1	23.2	6.68	6.50	8.33	6.94	6.13	6.41
16	4.33	4.42	4.70	7.90	10.2	41.0	6.68	5.84	8.42	6.94	5.84	6.50
17	3.75	4.52	4.98	6.13	8.81	22.5	6.59	5.65	9.09	6.94	6.23	6.50
18	3.46	4.52	6.13	6.23	7.90	17.1	6.32	6.04	8.23	6.41	6.50	6.50
19	4.04	4.89	12.9	6.50	10.1	12.6	6.13	6.04	7.68	6.13	6.50	6.23
20	4.23	5.55	12.2	6.32	28.6	10.7	6.59	6.13	7.03	6.59	6.50	6.04
21	4.23	4.89	8.61	10.2	26.8	9.39	6.59	5.94	6.76	6.76	6.41	6.41
22	4.33	4.14	6.59	15.7	23.7	8.81	6.59	5.45	7.03	6.85	6.13	6.59
23	4.23	4.61	5.75	8.90	18.0	8.61	6.59	4.98	7.03	6.85	5.75	6.76
24	3.85	5.26	5.26	7.79	15.5	8.33	6.41	5.07	7.03	6.68	6.13	6.85
25	3.65	6.32	4.98	6.94	14.1	8.61	6.04	5.75	6.85	6.32	6.41	6.85
26	4.23	7.45	4.61	5.26	14.0	12.2	5.84	5.94	6.76	6.04	6.41	6.59
27	4.33	6.50	5.26	4.52	21.0	11.0	6.23	5.94	6.32	6.41	6.50	6.85
28	4.42	5.55	5.84	4.70	34.6	9.00	6.32	5.94	6.13	6.59	6.41	8.71
29	4.23	5.07	6.94	5.55	-----	8.23	6.32	5.84	6.59	6.68	6.23	8.01
30	3.94	5.26	7.45	5.65	-----	8.12	6.32	5.36	6.68	6.59	6.13	7.34
31	3.65	-----	6.76	5.45	-----	8.01	-----	5.17	-----	6.59	6.50	-----
Maks.	5.75	7.90	15.6	19.4	41.2	41.5	8.01	6.94	110.	50.0	6.68	9.80
Min.	3.26	2.20	3.36	3.16	5.26	7.79	5.65	4.70	4.70	5.84	5.55	5.55
Ortalama	4.22	4.37	5.72	6.38	13.7	16.0	6.70	5.90	8.91	8.11	6.32	6.57
LT/SN/Km2	2.98	3.09	4.04	4.51	9.70	11.3	4.74	4.17	6.29	5.73	4.47	4.64
AKIM mm.	7.98	8.00	10.8	12.1	23.5	30.3	12.3	11.2	16.3	15.4	12.0	12.0
MİL. M3	11.3	11.3	15.3	17.1	33.2	42.9	17.4	15.8	23.1	21.7	16.9	17.0

SU YILI (2006) YILLIK TOPLAM AKIM 243.00 MİLYON M3 172 MM. 5.4 LT/SN/Km2

01. Meriç-Ergene Havzasi

D01A026 MERİÇ N. IPSALA GÜMRÜK KÖPRÜSÜ

YERİ : **TURK-YUNAN HUDUDU OLAN IPSALA GUMRUK KOPRUSU UZERİNDEDIR. G16**
26°19'10" Doğu - 40°56'24" Kuzey

YAĞIŞ ALANI : **50030,00 km2** **YAKLAŞIK KOT : 1 m**

GÖZLEM SÜRESİ : **01.01.1961 - 30.09.2006**

ORTALAMA AKIMLAR : **Gözlem süresinde 266.302 m3/sn. (10 Yıllık) 2006 Su yılında 391.456 m3/sn.**

ANLIK EN ÇOK VE EN AZ AKIMLAR:

2006 Su yılında anlık ençok akım	:	**2632**	**m3/sn**	**17.03.2006**
2006 Su yılında anlık enaz akım	:	**46.8**	**m3/sn**	**19.08.2006**
Gözlem süresinde anlık ençok akım	:	**2900**	**m3/sn**	**09.03.1971**
Gözlem süresinde anlık enaz akım	:	**10.0**	**m3/sn**	**24.08.1974**

İstasyon için kullanılmış anahtar bulunamadı.

Akımlar 01 Ekim 2005 'den 30 Eylül 2006' a kadar m3/sn olarak

Gün	Ekim	Kasım	Aralık	Ocak	Şubat	Mart	Nisan	Mayıs	Haziran	Temmuz	Ağustos	Eylül
01	217.	195.	383.	900.	310.	895.	921.	651.	175.	148.	69.2	97.9
02	204.	192.	319.	878.	284.	1015	869.	610.	153.	127.	65.1	107.
03	195.	197.	310.	872.	290.	1083	804.	503.	155.	142.	69.2	107.
04	185.	170.	289.	962.	317.	1115	764.	373.	140.	152.	70.2	97.9
05	217.	168.	274.	984.	314.	1112	742.	358.	137.	210.	77.3	91.7
06	269.	169.	289.	1091	322.	1096	722.	330.	130.	330.	95.9	90.7
07	320.	169.	292.	1099	305.	1099	712.	342.	127.	365.	80.4	89.8
08	313.	166.	316.	1093	310.	1134	717.	315.	154.	258.	87.9	85.1
09	313.	166.	293.	1083	308.	1107	689.	285.	193.	236.	72.2	80.4
10	262.	161.	246.	1056	299.	1162	659.	261.	260.	206.	64.1	85.1
11	219.	162.	246.	1018	304.	1178	649.	257.	271.	164.	67.1	81.4
12	242.	165.	240.	987.	301.	1282	659.	253.	248.	146.	72.2	80.4
13	239.	169.	245.	934.	301.	1427	666.	243.	254.	140.	77.3	87.0
14	266.	158.	233.	866.	320.	1745	679.	239.	257.	132.	73.2	87.0
15	204.	162.	238.	782.	316.	1907	679.	232.	274.	128.	69.2	100.
16	194.	174.	246.	716.	332.	2563	674.	217.	270.	110.	66.1	106.
17	184.	167.	286.	669.	334.	2593	659.	211.	243.	124.	55.2	106.
18	174.	158.	259.	621.	340.	1907	649.	199.	230.	140.	57.1	106.
19	174.	166.	280.	578.	366.	1848	636.	193.	216.	160.	49.5	105.
20	159.	153.	284.	536.	372.	1711	621.	180.	221.	154.	48.6	98.9
21	159.	171.	307.	506.	381.	1558	617.	165.	200.	132.	52.3	106.
22	158.	182.	331.	481.	405.	1475	617.	159.	174.	135.	54.2	113.
23	167.	176.	313.	474.	408.	1359	610.	158.	166.	130.	54.2	140.
24	181.	188.	317.	433.	405.	1426	610.	157.	166.	110.	52.3	162.
25	174.	299.	319.	403.	463.	1399	583.	156.	158.	88.8	66.1	154.
26	166.	388.	299.	400.	562.	1336	541.	171.	138.	78.3	72.2	134.
27	158.	438.	275.	391.	641.	1287	528.	162.	122.	73.2	74.3	138.
28	157.	463.	425.	401.	711.	1228	503.	150.	120.	71.2	79.4	180.
29	175.	460.	590.	420.	-----	1126	480.	146.	123.	70.2	98.9	201.
30	195.	422.	751.	367.	-----	1092	462.	148.	144.	72.2	102.	227.
31	198.	-----	892.	325.	-----	1027	-----	134.	-----	73.2	101.	-----
Maks.	326.	467.	911.	1110	801.	2632	932.	659.	288.	419.	106.	243.
Min.	155.	151.	216.	322.	278.	831.	460.	131.	114.	70.2	46.8	76.3
Ortalama	208.	219.	335.	720.	369.	1397	657.	257.	187.	149.	70.8	115.
LT/SN/Km2	4.15	4.38	6.70	14.4	7.37	27.9	13.1	5.13	3.74	2.97	1.41	2.30
AKIM mm.	11.1	11.4	17.9	38.6	17.8	74.8	34.1	13.7	9.70	7.95	3.79	5.95
MİL. M3	556.	568.	897.	1929	892.	3740	1704	688.	485.	398.	190.	298.

SU YILI (2006) YILLIK TOPLAM AKIM 12345.00 MİLYON M3 247 MM. 7.8 LT/SN/Km2

01. Meriç-Ergene Havzasi

D01A031 SOGUCAK D. SOGUCAK

YERİ : **PINARHISAR-VIZE YOLUNUN 12 KM.SINDEN SOLA AYRILAN SERGEN BUCAGI YOLUNUN 2.5 KM SINDEKI SOGUCAK KOYUNDEDIR.E18D2**
27°39'17" Doğu - 41°38'10" Kuzey

YAĞIŞ ALANI : **71,30 km2** **YAKLAŞIK KOT : 271 m**

GÖZLEM SÜRESİ : **09.07.1964 - 30.09.2006**

ORTALAMA AKIMLAR : **Gözlem süresinde 0.386 m3/sn. (42 Yıllık) 2006 Su yılında 0.794 m3/sn.**

ANLIK EN ÇOK VE EN AZ AKIMLAR:

2006 Su yılında anlık encok akım	**:**	**124.**	**m3/sn**	**02.07.2006**
2006 Su yılında anlık enaz akım	**:**	**0.049**	**m3/sn**	**21.09.2006**
Gözlem süresinde anlık encok akım	**:**	**210.**	**m3/sn**	**14.12.1973**
Gözlem süresinde anlık enaz akım	**:**	**0.001**	**m3/sn**	**23.07.1999**

İstasyon için kullanılmış anahtar bulunamadı.

Akımlar 01 Ekim 2005 'den 30 Eylül 2006' a kadar m3/sn olarak

Gün	Ekim	Kasım	Aralık	Ocak	Şubat	Mart	Nisan	Mayıs	Haziran	Temmuz	Ağustos	Eylül
01	0.060	0.098	0.320	0.964	0.396	1.50	0.964	0.517	0.290	0.517	1.35	0.768
02	0.142	0.098	0.320	0.768	0.396	1.27	0.964	0.517	0.290	3.24	1.35	0.768
03	0.098	0.098	0.270	0.638	0.396	1.65	0.964	0.517	0.290	14.6	1.35	0.768
04	0.060	0.098	0.270	0.577	0.396	1.20	0.899	0.517	0.290	5.92	1.35	0.768
05	0.060	0.098	0.270	0.517	0.396	1.20	0.834	0.517	0.290	2.30	1.35	0.768
06	0.060	0.098	0.270	0.517	0.396	1.20	0.768	0.456	0.244	2.15	1.35	0.768
07	0.060	0.098	0.270	0.517	0.396	2.56	0.768	0.456	0.199	2.15	1.35	0.768
08	0.060	0.098	0.270	0.517	0.396	1.98	0.768	0.456	0.456	2.15	1.35	0.703
09	0.060	0.098	0.270	0.517	0.396	1.72	0.768	0.456	3.84	1.98	1.35	0.638
10	0.060	0.098	0.270	0.517	0.456	1.81	0.768	0.456	1.20	1.98	1.35	0.638
11	0.060	0.098	0.270	0.456	0.577	3.08	0.768	0.456	0.768	1.89	1.35	0.638
12	0.060	0.098	0.270	0.396	0.517	4.18	0.768	0.456	0.768	1.81	1.35	0.638
13	0.060	0.098	0.270	0.396	0.517	2.40	0.703	0.456	0.768	1.81	1.35	0.638
14	0.060	0.098	0.270	0.396	0.396	2.72	0.703	0.456	0.768	1.72	1.35	0.638
15	0.060	0.098	0.320	0.290	0.396	2.40	0.638	0.456	0.768	1.65	1.35	0.517
16	0.060	0.098	0.320	0.290	0.396	2.20	0.638	0.456	0.703	1.57	1.35	0.244
17	0.060	0.200	0.320	0.290	0.577	1.81	0.638	0.396	0.703	1.57	1.35	0.199
18	0.060	0.200	0.580	0.335	1.35	1.57	0.638	0.396	0.703	1.57	1.35	0.108
19	0.060	0.320	0.460	0.768	1.27	1.50	0.638	0.396	0.703	1.57	1.35	0.108
20	0.060	0.320	0.320	0.638	1.50	1.50	0.638	0.396	0.703	1.57	1.35	0.108
21	0.098	0.270	0.320	0.396	1.42	1.35	0.638	0.396	0.703	1.57	1.35	0.049
22	0.098	0.270	0.320	0.396	1.57	1.35	0.638	0.396	0.638	1.57	1.35	0.049
23	0.098	0.200	0.320	0.290	1.35	1.35	0.517	0.396	0.638	1.57	1.35	0.049
24	0.098	0.390	0.320	0.199	1.04	1.50	0.517	0.335	0.638	1.57	1.35	0.049
25	0.098	0.980	0.320	0.199	1.20	1.35	0.517	0.290	0.638	1.57	1.27	0.049
26	0.098	0.520	0.320	0.244	2.06	1.20	0.517	0.290	0.577	1.50	0.834	0.049
27	0.098	0.460	0.795	0.335	1.89	1.20	0.517	0.290	0.517	1.42	0.768	0.049
28	0.098	0.320	1.79	0.396	1.57	1.12	0.517	0.290	0.517	1.35	0.768	0.049
29	0.098	0.320	1.30	0.396	-----	1.12	0.517	0.290	0.517	1.35	0.768	0.049
30	0.098	0.320	1.30	0.456	-----	1.04	0.517	0.290	0.517	1.35	0.768	0.049
31	0.098	-----	3.01	0.396	-----	0.964	-----	0.290	-----	1.35	0.768	-----
Maks.	0.200	1.25	7.40	1.04	2.94	7.40	0.964	0.517	9.46	124.	1.35	0.768
Min.	0.060	0.098	0.270	0.199	0.396	0.964	0.517	0.290	0.199	0.517	0.768	0.049
Ortalama	0.077	0.222	0.526	0.452	0.843	1.71	0.688	0.411	0.688	2.25	1.24	0.389
LT/SN/Km2	1.08	3.11	7.38	6.34	11.8	24.0	9.65	5.76	9.65	31.6	17.3	5.46
AKIM mm.	2.91	8.07	19.8	17.0	28.6	64.2	25.0	15.4	25.0	84.7	46.5	14.2
MİL. M3	0.207	0.575	1.41	1.21	2.04	4.58	1.78	1.10	1.78	6.04	3.31	1.01

SU YILI (2006) YILLIK TOPLAM AKIM 25.04 MİLYON M3 351 MM. 11.1 LT/SN/Km2

01. Meriç-Ergene Havzasi

D01A039 POYRALI D. POYRALI

YERİ : **PINARHISAR A 7 KM MESAFEDEKI POYRALI BUCAGININ 1.2 KM MENBAINDADIR.**
27°35'58" Doğu - 41°38'25" Kuzey

YAĞIŞ ALANI : **96,40 km2** **YAKLAŞIK KOT : 250 m**

GÖZLEM SÜRESİ : **01.10.1965 - 30.09.2006**

ORTALAMA AKIMLAR : **Gözlem süresinde 0.451 m3/sn. (41 Yıllık) 2006 Su yılında 0.991 m3/sn.**

ANLIK EN ÇOK VE EN AZ AKIMLAR:

2006 Su yılında anlık ençok akım	**:**	**176.**	**m3/sn**	**02.07.2006**
2006 Su yılında anlık enaz akım	**:**	**0.000**	**m3/sn**	**01.10.2005**
Gözlem süresinde anlık ençok akım	**:**	**185.**	**m3/sn**	**04.01.1966**
Gözlem süresinde anlık enaz akım	**:**	**0.000**	**m3/sn**	**01.10.1965**

İstasyon için kullanılmış anahtar bulunamadı.

Akımlar 01 Ekim 2005 'den 30 Eylül 2006' a kadar m3/sn olarak

Gün	Ekim	Kasım	Aralık	Ocak	Şubat	Mart	Nisan	Mayıs	Haziran	Temmuz	Ağustos	Eylül
01	KURU	KURU	KURU	0.800	0.975	4.85	0.800	0.200	KURU	10.1	0.004	0.004
02	KURU	KURU	KURU	0.620	0.975	5.50	0.800	0.080	KURU	113.	0.004	0.004
03	KURU	KURU	KURU	0.620	0.800	4.52	0.800	0.080	KURU	36.9	0.001	0.004
04	KURU	KURU	KURU	0.620	0.620	2.80	0.800	0.080	KURU	10.5	0.001	0.004
05	KURU	KURU	KURU	0.620	0.200	2.80	0.800	0.080	KURU	0.320	0.001	KURU
06	KURU	KURU	KURU	0.620	0.042	2.80	0.620	0.080	KURU	0.320	0.001	KURU
07	KURU	KURU	0.001	0.620	0.042	16.4	0.620	0.080	KURU	0.320	0.001	KURU
08	KURU	KURU	0.010	0.620	0.042	3.64	0.620	0.080	KURU	0.200	0.010	KURU
09	KURU	KURU	0.010	0.620	0.042	3.08	0.620	0.080	13.6	0.200	0.004	KURU
10	KURU	KURU	0.010	0.620	0.042	2.57	0.620	0.200	1.48	0.080	0.001	KURU
11	KURU	KURU	0.010	0.620	0.042	4.20	0.620	0.200	0.620	0.042	0.001	KURU
12	KURU	KURU	0.010	0.620	0.021	12.0	0.620	0.200	0.320	0.042	0.001	KURU
13	KURU	KURU	0.010	0.620	0.010	4.20	0.620	0.200	0.200	0.021	0.001	KURU
14	KURU	KURU	0.010	0.620	0.010	1.15	0.620	0.200	0.320	0.021	KURU	KURU
15	KURU	KURU	0.010	0.620	0.004	1.32	0.440	0.200	0.320	0.021	KURU	KURU
16	KURU	KURU	0.010	0.620	0.004	1.15	0.320	0.080	0.320	0.042	KURU	KURU
17	KURU	KURU	0.021	0.620	0.021	1.15	0.320	0.080	0.200	0.021	KURU	KURU
18	KURU	KURU	0.010	0.620	1.15	1.15	0.320	0.200	0.080	0.010	KURU	KURU
19	KURU	KURU	0.004	0.800	1.15	1.15	0.320	0.200	0.200	0.010	KURU	KURU
20	KURU	KURU	0.010	0.800	1.15	0.975	0.320	0.080	0.200	0.004	0.010	KURU
21	KURU	KURU	0.010	0.800	0.975	0.975	0.320	0.080	0.080	0.001	0.004	KURU
22	KURU	KURU	0.010	0.800	0.800	0.975	0.320	0.080	0.042	0.001	0.004	KURU
23	KURU	KURU	0.010	0.975	0.800	0.975	0.320	0.080	0.042	0.004	KURU	KURU
24	KURU	0.004	0.010	0.975	0.975	0.975	0.200	0.042	0.042	0.004	KURU	KURU
25	KURU	0.042	0.010	0.975	1.65	0.975	0.200	0.042	0.021	0.004	KURU	KURU
26	KURU	0.001	0.004	0.975	8.58	0.975	0.200	0.042	0.021	0.004	KURU	KURU
27	KURU	KURU	3.36	0.975	3.64	0.800	0.200	0.042	0.021	0.001	KURU	KURU
28	KURU	KURU	2.11	0.975	3.92	0.800	0.080	0.021	0.021	0.001	KURU	KURU
29	KURU	KURU	0.975	0.975	-----	0.800	0.200	0.010	0.021	0.004	0.010	KURU
30	KURU	KURU	1.32	0.975	-----	0.800	0.200	0.010	0.021	0.001	0.004	KURU
31	KURU	-----	6.89	0.975	-----	0.800	-----	0.001	-----	0.001	0.004	-----
Maks.	KURU	0.800	41.7	1.48	25.0	43.5	0.800	0.320	68.0	176.	0.021	0.004
Min.	KURU	KURU	KURU	0.440	0.004	0.800	0.080	KURU	KURU	KURU	KURU	KURU
Ortalama	KURU	0.002	0.479	0.752	1.02	2.81	0.462	0.101	0.606	5.55	0.002	0.001
LT/SN/Km2	0.000	0.016	4.97	7.80	10.6	29.2	4.79	1.05	6.29	57.6	0.022	0.006
AKIM mm.	0.000	0.042	13.3	20.9	25.7	78.2	12.4	2.81	16.3	154.	0.060	0.014
MİL. M3	0.000	0.004	1.28	2.01	2.48	7.54	1.20	0.270	1.57	14.9	0.006	0.001

SU YILI (2006) YILLIK TOPLAM AKIM 31.26 MİLYON M3 324 MM. 10.3 LT/SN/Km2

01. Meriç-Ergene Havzasi

D01A046 HAMZADERE KOCAHIDIR

YERİ : **KESAN-ENEZ YOLUNUN19 KM.DEKI KARAHISAR KOYUNDEN SAGA AYRILAN KARAYOLUNUN 10 KM.DEKI KOCAHIDIR KOYUNDEDIR.**
26°24'0" Doğu - 40°48'0" Kuzey

YAĞIŞ ALANI : **69,90 km2** **YAKLAŞIK KOT : 11 m**

GÖZLEM SÜRESİ : **16.11.1970 - 30.09.2006**

ORTALAMA AKIMLAR : **Gözlem süresinde 0.255 m3/sn. (34 Yıllık) 2006 Su yılında 0.456 m3/sn.**

ANLIK EN ÇOK VE EN AZ AKIMLAR:

2006 Su yılında anlık ençok akım	**:**	**119.**	**m3/sn**	**12.03.2006**
2006 Su yılında anlık enaz akım	**:**	**0.000**	**m3/sn**	**01.10.2005**
Gözlem süresinde anlık ençok akım	**:**	**175.**	**m3/sn**	**05.03.1981**
Gözlem süresinde anlık enaz akım	**:**	**0.000**	**m3/sn**	**01.07.1984**

İstasyon için kullanılmış anahtar bulunamadı.

Akımlar 01 Ekim 2005 'den 30 Eylül 2006' a kadar m3/sn olarak

Gün	Ekim	Kasım	Aralık	Ocak	Şubat	Mart	Nisan	Mayıs	Haziran	Temmuz	Ağustos	Eylül
01	KURU	KURU	0.080	0.200	0.017	0.130	0.450	0.360	0.270	0.270	KURU	KURU
02	KURU	KURU	0.080	0.200	0.004	0.130	0.450	0.360	0.270	0.360	KURU	KURU
03	KURU	KURU	0.080	3.60	KURU	4.50	0.450	0.360	0.270	1.25	KURU	KURU
04	KURU	KURU	0.080	2.20	KURU	0.450	0.450	0.360	0.270	0.450	KURU	KURU
05	KURU	KURU	0.080	0.360	KURU	0.450	0.450	0.360	0.270	0.270	KURU	KURU
06	KURU	KURU	0.080	11.0	0.004	0.360	0.450	0.360	0.270	0.270	KURU	KURU
07	KURU	KURU	0.080	3.20	0.004	7.50	0.450	0.360	0.270	0.270	KURU	KURU
08	KURU	KURU	0.080	0.650	0.004	3.50	0.450	0.270	0.450	0.270	KURU	KURU
09	KURU	KURU	0.080	0.080	0.017	2.00	0.450	0.270	0.450	0.270	KURU	KURU
10	KURU	KURU	0.080	0.080	0.017	1.15	0.450	0.270	0.270	0.270	KURU	KURU
11	KURU	KURU	0.080	0.080	0.017	2.90	0.450	0.450	0.270	0.270	KURU	KURU
12	KURU	KURU	0.080	0.080	0.004	28.0	0.450	0.750	0.270	0.270	KURU	KURU
13	KURU	KURU	0.080	0.080	0.004	5.30	0.450	0.650	0.270	0.270	KURU	KURU
14	KURU	KURU	0.080	0.080	0.004	3.10	0.450	0.360	0.270	0.017	KURU	KURU
15	KURU	KURU	0.080	0.080	0.004	2.40	0.450	0.360	0.270	0.017	KURU	KURU
16	KURU	KURU	0.080	0.080	0.004	2.70	0.450	0.360	0.550	0.017	KURU	KURU
17	KURU	KURU	0.080	0.080	1.60	0.450	0.450	0.360	0.270	0.017	KURU	KURU
18	KURU	KURU	8.60	0.080	2.30	0.450	0.450	0.550	0.270	0.017	KURU	KURU
19	KURU	KURU	0.650	0.080	0.004	0.450	0.450	0.550	0.270	0.017	KURU	KURU
20	KURU	KURU	0.080	0.080	0.004	0.450	0.450	0.360	1.15	0.017	KURU	KURU
21	KURU	KURU	0.080	0.080	0.004	0.450	0.450	0.360	0.360	0.017	KURU	KURU
22	KURU	KURU	0.080	0.080	0.004	0.450	0.450	0.360	0.270	0.017	KURU	KURU
23	KURU	KURU	0.080	0.080	0.004	0.450	0.450	0.360	0.270	0.004	KURU	KURU
24	KURU	KURU	0.080	0.080	0.004	0.450	0.450	0.360	0.270	0.004	KURU	KURU
25	KURU	3.60	0.080	0.080	2.20	0.450	0.450	0.270	0.270	0.004	KURU	KURU
26	KURU	0.200	0.080	0.080	3.80	0.450	0.450	0.270	0.270	0.004	KURU	KURU
27	KURU	2.80	0.450	0.080	0.200	0.450	0.450	0.270	0.270	KURU	KURU	KURU
28	KURU	0.080	0.750	0.080	0.130	0.450	0.550	0.270	0.270	KURU	KURU	KURU
29	KURU	0.080	0.080	0.080	-----	0.450	0.550	0.270	0.270	KURU	KURU	KURU
30	KURU	0.130	0.270	0.080	-----	0.450	0.450	0.270	0.270	KURU	KURU	KURU
31	KURU	-----	2.20	0.040	-----	0.450	-----	0.270	-----	KURU	KURU	-----
Maks.	KURU	9.80	42.0	31.0	10.5	119.	0.550	1.40	2.70	2.70	KURU	KURU
Min.	KURU	KURU	0.080	0.040	KURU	0.130	0.450	0.270	0.270	KURU	KURU	KURU
Ortalama	KURU	0.230	0.481	0.749	0.370	2.30	0.457	0.368	0.324	0.159	KURU	KURU
LT/SN/Km2	0.000	3.29	6.89	10.7	5.29	32.9	6.53	5.27	4.63	2.27	0.000	0.000
AKIM mm.	0.000	8.52	18.4	28.7	12.8	88.2	16.9	14.1	12.0	6.09	0.000	0.000
MİL. M3	0.000	0.595	1.29	2.01	0.895	6.16	1.18	0.986	0.839	0.426	0.000	0.000

SU YILI (2006) YILLIK TOPLAM AKIM 14.38 MİLYON M3 206 MM. 6.5 LT/SN/Km2

01. Meriç-Ergene Havzasi

D01A055 PRAVADİ D. HASANAĞA KÖYÜ

YERİ : 1983EDIRNE-HASANAGA KOYUNDEDIR.
26°37'0" Doğu - 41°43'0" Kuzey

YAĞIŞ ALANI : 198,30 km2 **YAKLAŞIK KOT :** 55 m

GÖZLEM SÜRESİ : 22.09.1982 - 30.09.2006

ORTALAMA AKIMLAR : Gözlem süresinde 0.350 m3/sn. (24 Yıllık) 2006 Su yılında 0.579 m3/sn.

ANLIK EN ÇOK VE EN AZ AKIMLAR:

2006 Su yılında anlık ençok akım	:	76.0	m3/sn	12.03.2006
2006 Su yılında anlık enaz akım	:	0.000	m3/sn	09.07.2006
Gözlem süresinde anlık ençok akım	:	96.8	m3/sn	27.02.2005
Gözlem süresinde anlık enaz akım	:	0.000	m3/sn	27.07.1983

İstasyon için kullanılmış anahtar bulunamadı.

Akımlar 01 Ekim 2005 'den 30 Eylül 2006' a kadar m3/sn olarak

Gün	Ekim	Kasım	Aralık	Ocak	Şubat	Mart	Nisan	Mayıs	Haziran	Temmuz	Ağustos	Eylül
01	0.031	0.085	0.205	0.440	0.406	1.73	0.716	0.473	0.171	0.102	KURU	KURU
02	0.028	0.085	0.239	0.440	0.406	0.980	0.716	0.440	0.171	0.102	KURU	KURU
03	0.028	0.085	0.272	1.91	0.406	0.804	0.716	0.406	0.171	0.102	KURU	KURU
04	0.028	0.085	0.272	2.71	0.406	0.760	0.716	0.373	0.171	0.085	KURU	KURU
05	0.031	0.085	0.239	1.82	0.406	0.716	0.716	0.339	0.154	0.085	KURU	KURU
06	0.051	0.085	0.239	2.53	0.473	0.716	0.716	0.306	0.154	0.051	KURU	KURU
07	0.068	0.102	0.205	2.17	0.540	0.760	0.672	0.272	0.154	0.015	KURU	KURU
08	0.068	0.102	0.306	1.55	0.540	1.73	0.672	0.205	0.154	KURU	KURU	KURU
09	0.068	0.102	0.540	1.27	0.540	1.44	0.672	0.205	0.137	KURU	KURU	KURU
10	0.085	0.102	0.440	1.04	0.628	0.804	0.672	0.205	0.137	KURU	KURU	KURU
11	0.102	0.102	0.406	0.892	0.628	1.09	0.672	0.205	0.137	KURU	KURU	KURU
12	0.102	0.120	0.373	0.804	0.628	34.8	0.628	0.205	0.120	KURU	KURU	KURU
13	0.102	0.120	0.339	0.760	0.628	16.3	0.628	0.205	0.120	KURU	KURU	KURU
14	0.102	0.120	0.339	0.716	0.540	5.00	0.584	0.205	0.120	KURU	KURU	KURU
15	0.102	0.137	0.339	0.628	0.540	4.42	0.584	0.205	0.137	KURU	KURU	KURU
16	0.120	0.154	0.306	0.540	0.540	3.69	0.584	0.205	0.137	KURU	KURU	KURU
17	0.120	0.188	0.272	0.540	3.69	2.17	0.540	0.205	0.154	KURU	KURU	KURU
18	0.120	0.205	0.339	0.507	16.6	1.44	0.540	0.205	0.171	KURU	KURU	KURU
19	0.120	0.272	0.339	0.473	2.89	1.09	0.540	0.272	0.154	KURU	KURU	KURU
20	0.137	0.760	0.306	0.473	0.760	0.980	0.540	0.272	0.154	KURU	KURU	KURU
21	0.137	0.272	0.306	0.406	0.716	1.04	0.540	0.239	0.154	KURU	KURU	KURU
22	0.137	0.188	0.339	0.406	0.672	1.09	0.507	0.239	0.154	KURU	KURU	KURU
23	0.137	0.188	0.339	0.406	0.628	1.09	0.507	0.205	0.137	KURU	KURU	KURU
24	0.137	0.406	0.339	0.406	0.540	1.09	0.473	0.205	0.137	KURU	KURU	KURU
25	0.137	1.21	0.339	0.406	0.584	1.04	0.473	0.205	0.137	KURU	KURU	KURU
26	0.137	1.04	0.339	0.406	0.804	0.980	0.473	0.188	0.120	KURU	KURU	KURU
27	0.154	0.473	0.473	0.406	1.55	0.980	0.473	0.188	0.120	KURU	KURU	KURU
28	0.154	0.339	1.49	0.406	1.09	0.936	0.473	0.188	0.102	KURU	KURU	KURU
29	0.120	0.306	1.15	0.406	-----	0.848	0.473	0.171	0.102	KURU	KURU	KURU
30	0.102	0.239	0.804	0.406	-----	0.804	0.473	0.171	0.102	KURU	KURU	0.120
31	0.085	-----	0.507	0.406	-----	0.760	-----	0.171	-----	KURU	KURU	-----
Maks.	0.154	1.73	1.91	3.78	33.3	76.0	0.716	0.473	0.171	0.102	KURU	0.306
Min.	0.028	0.085	0.205	0.406	0.406	0.716	0.473	0.171	0.102	KURU	KURU	KURU
Ortalama	0.098	0.259	0.411	0.861	1.38	2.97	0.590	0.244	0.141	0.017	KURU	0.004
LT/SN/Km2	0.496	1.30	2.07	4.34	6.98	15.0	2.97	1.23	0.713	0.088	0.000	0.020
AKIM mm.	1.33	3.38	5.55	11.6	16.9	40.1	7.71	3.30	1.85	0.236	0.000	0.052
MİL. M3	0.264	0.670	1.10	2.31	3.35	7.96	1.53	0.655	0.367	0.047	0.000	0.010

SU YILI (2006) YILLIK TOPLAM AKIM 18.26 MİLYON M3 92 MM. 2.9 LT/SN/Km2

01. Meriç-Ergene Havzasi

D01A057 MERİÇ N. FERRE KUPURU

YERİ : **IPSALA-YENIKARPUZLU KOYUNUN 6 KM BATISINDA FERRE KUPURUNDEDIR. G16A3**
26°14'20" Doğu - 40°51'50" Kuzey

YAĞIŞ ALANI : **50140,00 km2** **YAKLAŞIK KOT : 1 m**

GÖZLEM SÜRESİ : **09.10.1985 - 30.09.2006**

ORTALAMA AKIMLAR : **Gözlem süresinde 174.455 m3/sn. (21 Yıllık) 2006 Su yılında 380.092 m3/sn.**

ANLIK EN ÇOK VE EN AZ AKIMLAR:

2006 Su yılında anlık ençok akım	**:**	**1926**	**m3/sn**	**15.03.2006**
2006 Su yılında anlık enaz akım	**:**	**60.6**	**m3/sn**	**24.08.2006**
Gözlem süresinde anlık ençok akım	**:**	**1926**	**m3/sn**	**15.03.2006**
Gözlem süresinde anlık enaz akım	**:**	**0.000**	**m3/sn**	**30.06.1987**

İstasyon için kullanılmış anahtar bulunamadı.

Akımlar 01 Ekim 2005 'den 30 Eylül 2006' a kadar m3/sn olarak

Gün	Ekim	Kasım	Aralık	Ocak	Şubat	Mart	Nisan	Mayıs	Haziran	Temmuz	Ağustos	Eylül
01	177.	205.	378.	848.	314.	784.	823.	565.	143.	149.	85.5	98.2
02	217.	200.	361.	800.	305.	964.	804.	537.	144.	128.	87.9	100.
03	205.	206.	346.	792.	290.	1070	791.	487.	139.	134.	90.4	103.
04	187.	162.	338.	970.	317.	1110	783.	392.	137.	142.	93.7	97.1
05	239.	158.	331.	1014	316.	1120	772.	377.	128.	204.	100.	94.9
06	323.	160.	338.	1240	321.	1110	757.	348.	117.	332.	111.	90.4
07	398.	160.	356.	1264	307.	1100	745.	329.	114.	377.	103.	87.9
08	386.	154.	391.	1248	309.	1130	749.	313.	136.	280.	104.	87.9
09	354.	154.	359.	1224	310.	1120	724.	287.	174.	238.	96.0	83.0
10	312.	147.	286.	1151	302.	1137	719.	274.	248.	207.	91.5	79.4
11	244.	148.	286.	1075	307.	1172	724.	267.	274.	159.	97.1	76.9
12	279.	153.	277.	1019	305.	1216	732.	260.	246.	142.	91.5	76.9
13	276.	160.	209.	920.	302.	1336	717.	246.	250.	137.	92.6	78.1
14	319.	141.	265.	784.	321.	1641	749.	248.	257.	127.	91.5	80.6
15	217.	148.	272.	690.	302.	1862	770.	239.	273.	126.	85.5	93.7
16	202.	154.	286.	630.	333.	1724	772.	228.	280.	113.	79.4	102.
17	186.	157.	348.	628.	340.	1706	770.	223.	250.	120.	75.6	102.
18	168.	141.	307.	615.	342.	1522	749.	211.	230.	133.	78.1	105.
19	143.	146.	340.	563.	362.	1352	741.	211.	215.	149.	73.1	108.
20	143.	132.	346.	508.	367.	1200	720.	202.	204.	143.	75.6	107.
21	141.	164.	378.	470.	374.	1085	711.	198.	200.	126.	81.8	110.
22	157.	181.	412.	437.	390.	1003	706.	190.	169.	126.	81.8	114.
23	157.	172.	386.	437.	390.	959.	708.	183.	160.	130.	80.6	128.
24	180.	192.	393.	434.	390.	931.	702.	174.	159.	114.	79.4	156.
25	168.	279.	394.	399.	425.	926.	684.	184.	156.	97.1	83.0	150.
26	154.	383.	367.	396.	515.	900.	644.	180.	136.	86.7	89.2	136.
27	141.	444.	333.	386.	584.	874.	620.	165.	121.	83.0	92.6	139.
28	140.	482.	425.	372.	640.	866.	591.	162.	121.	85.5	99.3	178.
29	169.	477.	577.	369.	-----	852.	563.	153.	124.	81.8	110.	202.
30	205.	420.	687.	364.	-----	841.	565.	155.	146.	86.7	114.	228.
31	208.	-----	824.	328.	-----	837.	-----	155.	-----	89.2	105.	-----
Maks.	406.	489.	872.	1296	699.	1926	829.	573.	294.	397.	125.	243.
Min.	136.	130.	209.	324.	279.	699.	547.	153.	110.	71.9	60.6	66.9
Ortalama	219.	213.	374.	722.	360.	1144	720.	263.	182.	150.	91.0	113.
LT/SN/Km2	4.37	4.24	7.46	14.4	7.18	22.8	14.4	5.24	3.62	2.99	1.81	2.26
AKIM mm.	11.7	11.0	20.0	38.6	17.4	61.1	37.2	14.0	9.39	8.01	4.86	5.85
MİL. M3	587.	551.	1002	1933	871.	3063	1867	704.	471.	401.	244.	293.

SU YILI (2006) YILLIK TOPLAM AKIM 11987.00 MİLYON M3 239 MM. 7.6 LT/SN/Km2

01. Meriç-Ergene Havzasi

D01A062 FİSINE D. B.ISMAİLCE

YERİ : **EDİRNE B ISMAILCE-YOLUSTU KOYLERI ARASINDA YAKLASIK 4.5 KMSINDEKI KOPRU UZERINDEDIR E17A4**
26°31'10" Doğu - 41°48'30" Kuzey

YAĞIŞ ALANI : **136,00 km2** **YAKLAŞIK KOT : 55 m**

GÖZLEM SÜRESİ : **01.01.1988 - 30.09.2006**

ORTALAMA AKIMLAR : **Gözlem süresinde 0.315 m3/sn. (18 Yıllık) 2006 Su yılında 0.534 m3/sn.**

ANLIK EN ÇOK VE EN AZ AKIMLAR:

2006 Su yılında anlık encok akım	**:**	**50.0**	**m3/sn**	**12.03.2006**
2006 Su yılında anlık enaz akım	**:**	**0.000**	**m3/sn**	**29.07.2006**
Gözlem süresinde anlık encok akım	**:**	**60.5**	**m3/sn**	**23.02.1996**
Gözlem süresinde anlık enaz akım	**:**	**0.000**	**m3/sn**	**17.07.1988**

İstasyon için kullanılmış anahtar bulunamadı.

Akımlar 01 Ekim 2005 'den 30 Eylül 2006' a kadar m3/sn olarak

Gün	Ekim	Kasım	Aralık	Ocak	Şubat	Mart	Nisan	Mayıs	Haziran	Temmuz	Ağustos	Eylül
01	0.265	0.312	0.616	0.507	0.242	4.98	0.369	0.219	0.022	0.044	KURU	KURU
02	0.242	0.369	0.616	0.473	0.242	1.80	0.369	0.219	0.017	0.044	KURU	KURU
03	0.219	0.404	0.616	0.561	0.219	1.13	0.335	0.200	0.096	0.035	KURU	KURU
04	0.219	0.369	0.561	0.996	0.242	0.724	0.335	0.180	0.265	0.031	KURU	KURU
05	0.180	0.265	0.473	1.65	0.219	0.473	0.312	0.180	0.219	0.031	KURU	KURU
06	0.141	0.180	0.369	7.60	0.219	0.670	0.312	0.180	0.200	0.031	KURU	KURU
07	0.109	0.161	0.335	4.45	0.242	2.10	0.312	0.161	0.200	0.027	KURU	KURU
08	0.084	0.161	0.438	1.65	0.242	2.00	0.670	0.161	0.404	0.027	KURU	KURU
09	0.071	0.161	1.28	1.43	0.242	1.58	0.779	0.141	0.438	0.031	KURU	KURU
10	0.058	0.180	0.670	1.20	0.242	1.73	0.507	0.141	0.289	0.031	KURU	KURU
11	0.058	0.180	0.369	0.996	0.289	2.61	0.438	0.141	0.242	0.027	KURU	KURU
12	0.071	0.200	0.369	0.833	0.335	28.6	0.369	0.161	0.219	0.027	KURU	KURU
13	0.058	0.219	0.335	0.670	0.312	14.4	0.404	0.161	0.180	0.031	KURU	KURU
14	0.096	0.219	0.312	0.507	0.265	4.77	0.369	0.050	0.161	0.031	KURU	KURU
15	0.122	0.242	0.312	0.438	0.242	3.32	0.369	0.122	0.141	0.031	KURU	KURU
16	0.096	0.265	0.312	0.404	0.312	2.71	0.335	0.141	0.141	0.031	KURU	KURU
17	0.084	0.265	0.335	0.369	0.670	2.10	0.335	0.180	0.109	0.027	KURU	KURU
18	0.096	0.265	0.335	0.369	0.887	1.65	0.312	0.289	0.071	0.027	KURU	KURU
19	0.096	0.289	0.335	0.369	0.779	1.43	0.335	0.265	0.058	0.022	KURU	KURU
20	0.084	0.312	0.335	0.404	0.616	1.13	0.335	0.242	0.058	0.022	KURU	KURU
21	0.084	0.438	0.312	0.335	0.507	1.05	0.312	0.219	0.050	0.022	KURU	KURU
22	0.071	0.404	0.312	0.335	0.438	0.996	0.312	0.200	0.044	0.017	KURU	KURU
23	0.071	0.369	0.312	0.312	0.404	0.887	0.289	0.122	0.035	0.017	KURU	KURU
24	0.084	0.561	0.289	0.312	0.404	0.833	0.289	0.096	0.035	0.022	KURU	KURU
25	0.096	3.32	0.312	0.289	1.43	0.779	0.265	0.058	0.035	0.017	KURU	KURU
26	0.141	2.91	0.289	0.265	3.21	0.724	0.242	0.044	0.031	0.017	KURU	KURU
27	0.369	1.65	0.369	0.265	3.52	0.670	0.242	0.031	0.031	0.009	KURU	KURU
28	0.404	1.35	2.91	0.289	2.00	0.561	0.219	0.031	0.031	0.007	KURU	KURU
29	0.369	0.616	1.58	0.289	-----	0.507	0.219	0.031	0.035	KURU	KURU	KURU
30	0.335	0.616	0.887	0.242	-----	0.473	0.219	0.027	0.044	KURU	KURU	KURU
31	0.312	-----	0.670	0.219	-----	0.438	-----	0.027	-----	KURU	KURU	-----
Maks.	0.404	3.82	4.45	14.6	8.46	50.0	1.05	0.312	0.616	0.044	KURU	KURU
Min.	0.058	0.141	0.265	0.219	0.219	0.404	0.219	0.022	0.017	KURU	KURU	KURU
Ortalama	0.154	0.575	0.567	0.936	0.678	2.83	0.350	0.143	0.130	0.024	KURU	KURU
LT/SN/Km2	1.13	4.23	4.17	6.89	4.98	20.8	2.58	1.05	0.956	0.175	0.000	0.000
AKIM mm.	3.04	11.0	11.2	18.4	12.1	55.8	6.68	2.81	2.48	0.468	0.000	0.000
MİL. M3	0.413	1.49	1.52	2.51	1.64	7.59	0.908	0.382	0.337	0.064	0.000	0.000

SU YILI (2006) YILLIK TOPLAM AKIM 16.85 MİLYON M3 124 MM. 3.9 LT/SN/Km2

01. Meriç-Ergene Havzasi

D01A063 AYVACIK D. AYVACIK

YERİ : 1989T.DAG-SARAY-AYVACIK KOY YOLUNUN AYVACIK A 1.5 KM MESAFEDEDIR F19B2
27°56'40" Doğu - 41°29'50" Kuzey

YAĞIŞ ALANI : 25,80 km2 **YAKLAŞIK KOT :** 183 m

GÖZLEM SÜRESİ : 01.10.1987 - 30.09.2006

ORTALAMA AKIMLAR : Gözlem süresinde 0.287 m3/sn. (19 Yıllık) 2006 Su yılında 0.549 m3/sn.

ANLIK EN ÇOK VE EN AZ AKIMLAR:

2006 Su yılında anlık ençok akım	:	12.5	m3/sn	09.06.2006
2006 Su yılında anlık enaz akım	:	0.000	m3/sn	12.09.2006
Gözlem süresinde anlık ençok akım	:	35.5	m3/sn	17.12.1988
Gözlem süresinde anlık enaz akım	:	0.000	m3/sn	27.07.1989

İstasyon için kullanılmış anahtar bulunamadı.

Akımlar 01 Ekim 2005 'den 30 Eylül 2006' a kadar m3/sn olarak

Gün	Ekim	Kasım	Aralık	Ocak	Şubat	Mart	Nisan	Mayıs	Haziran	Temmuz	Ağustos	Eylül
01	0.020	0.193	0.193	2.30	1.79	2.10	0.398	0.035	0.009	0.160	0.002	0.002
02	0.060	0.193	0.135	1.14	1.73	1.43	0.361	0.035	0.009	0.361	0.002	0.002
03	0.135	0.226	0.135	0.740	1.61	1.73	0.361	0.035	0.009	2.60	0.003	0.002
04	0.027	0.226	0.110	0.605	1.49	1.25	0.325	0.035	0.009	0.885	0.003	0.002
05	0.020	0.226	0.085	0.695	1.37	0.933	0.325	0.035	0.009	0.398	0.003	0.002
06	0.027	0.226	0.085	0.788	1.25	0.788	0.292	0.035	0.027	0.292	0.003	0.001
07	0.035	0.226	0.060	0.740	1.25	2.50	0.259	0.035	0.027	0.226	0.002	KURU
08	0.035	0.110	0.160	0.605	1.25	2.35	0.259	0.060	0.695	0.193	0.002	KURU
09	0.035	0.160	0.226	0.470	1.31	1.73	0.259	0.193	8.50	0.160	0.002	KURU
10	0.035	0.193	0.160	0.361	2.30	1.79	0.259	0.160	2.20	0.135	0.002	KURU
11	0.035	0.193	0.110	0.325	2.65	2.45	0.259	0.135	0.885	0.135	0.001	KURU
12	0.060	0.193	0.085	0.325	2.60	3.20	0.259	0.085	0.605	0.135	0.001	KURU
13	0.085	0.226	0.085	0.361	1.95	2.10	0.226	0.060	0.434	0.135	0.001	KURU
14	0.085	0.292	0.060	0.325	1.43	2.50	0.193	0.035	0.560	0.110	0.001	KURU
15	0.060	0.226	0.060	0.325	1.20	2.65	0.160	0.035	0.837	0.110	0.001	KURU
16	0.085	0.135	0.110	0.398	0.982	1.79	0.135	0.035	0.695	0.110	0.001	KURU
17	0.085	0.085	0.226	0.740	1.37	1.31	0.135	0.027	0.650	0.085	0.001	KURU
18	0.085	0.226	1.20	0.982	4.10	1.09	0.135	0.027	0.650	0.035	0.001	KURU
19	0.085	0.361	1.09	3.45	3.40	0.885	0.110	0.027	0.650	0.020	0.001	KURU
20	0.110	0.398	0.788	2.70	3.90	0.740	0.085	0.027	0.515	0.020	0.001	KURU
21	0.110	0.259	0.605	1.95	3.00	0.650	0.085	0.027	0.398	0.009	0.001	0.002
22	0.110	0.160	0.515	1.55	2.90	0.560	0.060	0.027	0.361	0.009	KURU	0.006
23	0.110	0.160	0.434	1.43	2.40	0.560	0.035	0.027	0.292	0.006	KURU	0.006
24	0.110	0.837	0.398	1.14	2.00	1.61	0.035	0.027	0.259	0.006	KURU	0.009
25	0.110	0.982	0.361	0.982	2.45	1.20	0.035	0.027	0.226	0.005	KURU	0.020
26	0.135	1.20	0.361	1.03	4.00	0.788	0.035	0.020	0.226	0.005	KURU	0.020
27	0.135	1.03	1.79	1.14	2.35	0.740	0.035	0.020	0.193	0.005	KURU	0.020
28	0.135	0.560	2.40	1.31	1.67	0.650	0.035	0.020	0.193	0.003	KURU	0.020
29	0.160	0.361	1.31	1.55	-----	0.560	0.035	0.020	0.160	0.002	0.001	0.060
30	0.160	0.226	1.03	1.73	-----	0.515	0.035	0.012	0.160	0.002	0.001	0.085
31	0.193	-----	2.35	1.85	-----	0.470	-----	0.009	-----	0.002	0.003	-----
Maks.	0.193	1.25	2.55	4.80	5.96	4.62	0.398	0.259	12.5	3.90	0.003	0.085
Min.	0.020	0.060	0.060	0.325	0.933	0.470	0.035	0.009	0.009	0.002	0.001	KURU
Ortalama	0.086	0.336	0.539	1.10	2.13	1.41	0.174	0.045	0.681	0.205	0.001	0.009
LT/SN/Km2	3.34	13.0	20.9	42.6	82.6	54.5	6.74	1.73	26.4	7.95	0.050	0.335
AKIM mm.	8.95	33.8	56.0	114.	200.	146.	17.5	4.64	68.5	21.3	0.134	0.867
MİL. M3	0.231	0.872	1.44	2.94	5.16	3.77	0.451	0.120	1.77	0.549	0.003	0.022

SU YILI (2006) YILLIK TOPLAM AKIM 17.33 MİLYON M3 672 MM. 21.3 LT/SN/Km2

01. Meriç-Ergene Havzasi

D01A065 ÇAYIR D. ÇAYIRDEREKÖY

YERİ : **ÇAYIRDERE KÖYÜNÜN 1.5 KM KUZEY DOĞUSUNDA KÖPRÜDEDİR. E19D1**
27°31'50" Doğu - 41°42'30" Kuzey

YAĞIŞ ALANI : **50,50 km2** **YAKLAŞIK KOT : 243 m**

GÖZLEM SÜRESİ : **21.09.1989 - 30.09.2006**

ORTALAMA AKIMLAR : **Gözlem süresinde 0.303 m3/sn. (17 Yıllık) 2006 Su yılında 0.428 m3/sn.**

ANLIK EN ÇOK VE EN AZ AKIMLAR:

2006 Su yılında anlık ençok akım	**:**	**48.0**	**m3/sn**	**09.06.2006**
2006 Su yılında anlık enaz akım	**:**	**0.001**	**m3/sn**	**27.08.2006**
Gözlem süresinde anlık ençok akım	**:**	**57.0**	**m3/sn**	**05.02.2003**
Gözlem süresinde anlık enaz akım	**:**	**0.000**	**m3/sn**	**01.10.1989**

İstasyon için kullanılmış anahtar bulunamadı.

Akımlar 01 Ekim 2005 'den 30 Eylül 2006' a kadar m3/sn olarak

Gün	Ekim	Kasım	Aralık	Ocak	Şubat	Mart	Nisan	Mayıs	Haziran	Temmuz	Ağustos	Eylül
01	0.044	0.058	0.142	1.05	0.704	2.09	0.558	0.257	0.122	0.142	0.044	0.044
02	0.161	0.058	0.142	0.777	0.668	1.60	0.522	0.257	0.122	1.05	0.044	0.044
03	0.090	0.058	0.142	0.850	0.558	1.53	0.522	0.257	0.122	2.90	0.044	0.044
04	0.058	0.058	0.142	0.777	0.522	0.558	0.522	0.257	0.122	1.05	0.044	0.034
05	0.044	0.058	0.142	0.631	0.485	1.05	0.522	0.257	0.122	0.370	0.044	0.034
06	0.044	0.058	0.122	1.18	0.595	1.00	0.485	0.257	0.122	0.313	0.044	0.022
07	0.044	0.058	0.103	0.900	0.777	5.77	0.485	0.257	0.122	0.285	0.044	0.014
08	0.044	0.058	0.103	0.668	0.704	2.27	0.456	0.257	0.285	0.257	0.044	0.014
09	0.044	0.058	0.122	0.558	0.741	1.71	0.456	0.257	3.34	0.257	0.044	0.014
10	0.044	0.058	0.142	0.522	0.950	1.45	0.456	0.257	0.485	0.257	0.044	0.022
11	0.044	0.058	0.161	0.485	0.704	2.36	0.456	0.257	0.285	0.228	0.044	0.022
12	0.058	0.058	0.181	0.485	0.558	3.42	0.456	0.257	0.257	0.200	0.034	0.022
13	0.058	0.058	0.161	0.485	0.522	1.91	0.456	0.257	0.257	0.200	0.034	0.022
14	0.058	0.058	0.142	0.485	0.485	2.00	0.456	0.257	0.257	0.181	0.034	0.022
15	0.058	0.074	0.200	0.456	0.485	1.75	0.456	0.257	0.257	0.181	0.034	0.022
16	0.058	0.074	0.257	0.428	0.485	1.64	0.428	0.257	0.228	0.161	0.022	0.022
17	0.058	0.200	0.228	0.399	0.485	1.22	0.428	0.257	0.228	0.161	0.022	0.022
18	0.058	0.228	0.257	0.456	0.668	1.18	0.428	0.228	0.200	0.161	0.022	0.022
19	0.058	0.342	0.313	0.814	1.60	1.09	0.399	0.228	0.181	0.142	0.022	0.022
20	0.058	0.200	0.342	0.777	1.75	1.00	0.370	0.200	0.181	0.122	0.022	0.022
21	0.044	0.142	0.370	0.704	1.60	0.950	0.342	0.181	0.181	0.103	0.022	0.044
22	0.044	0.103	0.313	0.595	1.38	0.900	0.342	0.181	0.181	0.090	0.014	0.034
23	0.044	0.103	0.257	0.456	1.18	0.850	0.313	0.181	0.161	0.090	0.014	0.142
24	0.044	0.631	0.257	0.399	1.09	0.814	0.313	0.161	0.161	0.090	0.014	0.058
25	0.044	1.13	0.228	0.522	1.53	0.741	0.313	0.161	0.161	0.074	0.009	0.034
26	0.044	0.428	0.200	1.22	2.72	0.704	0.285	0.161	0.161	0.058	0.003	0.034
27	0.044	0.285	1.82	1.45	1.78	0.668	0.285	0.161	0.161	0.058	0.003	0.044
28	0.044	0.228	2.63	0.900	2.27	0.631	0.285	0.161	0.142	0.058	0.014	0.044
29	0.044	0.200	1.75	0.850	-----	0.631	0.257	0.142	0.142	0.058	0.122	0.342
30	0.058	0.161	1.30	0.814	-----	0.595	0.257	0.142	0.142	0.044	0.074	0.200
31	0.058	-----	2.00	0.741	-----	0.558	-----	0.122	-----	0.044	0.058	-----
Maks.	0.200	1.26	33.6	2.00	7.94	22.1	0.558	0.285	48.0	27.8	0.161	0.950
Min.	0.034	0.058	0.103	0.399	0.485	0.558	0.257	0.122	0.122	0.044	0.001	0.014
Ortalama	0.055	0.178	0.473	0.704	1.000	1.44	0.410	0.219	0.296	0.303	0.035	0.049
LT/SN/Km2	1.08	3.53	9.37	13.9	19.8	28.5	8.12	4.33	5.87	5.99	0.688	0.978
AKIM mm.	2.90	9.14	25.1	37.4	47.9	76.4	21.1	11.6	15.2	16.1	1.84	2.54
MİL. M3	0.146	0.461	1.27	1.89	2.42	3.86	1.06	0.586	0.768	0.811	0.093	0.128

SU YILI (2006) YILLIK TOPLAM AKIM 13.49 MİLYON M3 267 MM. 8.5 LT/SN/Km2

01. Meriç-Ergene Havzasi

D01A069 DOLAPDERE ISLAMBEYLİ

YERİ : **ISLAMBEYLI-EVCILER KOYU ARASI YAKLASIK 2 KM SONRAKI KOPRUDEN SAGA SAPINCA 100 M ILERIDE SOL SAHILDEDIR. E19D1**
27°36'50" Doğu - 41°43'10" Kuzey

YAĞIŞ ALANI : **10,70 km2** **YAKLAŞIK KOT : 345 m**

GÖZLEM SÜRESİ : **22.11.2002 -**

ORTALAMA AKIMLAR : **Gözlem süresinde 0.113 m3/sn. (3 Yıllık) 2006 Su yılında 0.146 m3/sn.**

ANLIK EN ÇOK VE EN AZ AKIMLAR:

2006 Su yılında anlık encok akım	:	**3.70**	**m3/sn**	**02.07.2006**
2006 Su yılında anlık enaz akım	:	**0.002**	**m3/sn**	**01.10.2005**
Gözlem süresinde anlık encok akım	:	**3.70**	**m3/sn**	**02.07.2006**
Gözlem süresinde anlık enaz akım	:	**0.002**	**m3/sn**	**01.10.2003**

İstasyon için kullanılmış anahtar bulunamadı.

Akımlar 01 Ekim 2005 'den 30 Eylül 2006' a kadar m3/sn olarak

Gün	Ekim	Kasım	Aralık	Ocak	Şubat	Mart	Nisan	Mayıs	Haziran	Temmuz	Ağustos	Eylül
01	0.002	0.005	0.009	0.320	0.050	0.640	0.212	0.190	0.170	0.170	0.046	0.024
02	0.002	0.005	0.009	0.234	0.035	0.460	0.212	0.190	0.170	1.12	0.046	0.024
03	0.002	0.007	0.009	0.190	0.030	0.570	0.212	0.190	0.170	0.482	0.046	0.024
04	0.002	0.007	0.009	0.150	0.090	0.400	0.212	0.190	0.170	0.129	0.046	0.024
05	0.002	0.007	0.009	0.130	0.090	0.360	0.212	0.190	0.170	0.053	0.046	0.024
06	0.002	0.007	0.009	0.234	0.190	0.320	0.212	0.190	0.170	0.053	0.046	0.024
07	0.002	0.007	0.011	0.234	0.620	0.760	0.212	0.190	0.170	0.053	0.046	0.024
08	0.002	0.009	0.013	0.170	0.640	0.580	0.212	0.190	0.170	0.053	0.046	0.024
09	0.002	0.009	0.013	0.150	0.640	0.490	0.212	0.190	0.170	0.053	0.046	0.024
10	0.002	0.007	0.011	0.130	0.640	0.460	0.212	0.190	0.170	0.053	0.039	0.017
11	0.002	0.007	0.015	0.110	0.620	0.620	0.212	0.190	0.170	0.053	0.039	0.017
12	0.002	0.007	0.020	0.110	0.380	0.920	0.212	0.190	0.170	0.053	0.039	0.017
13	0.003	0.007	0.015	0.110	0.020	0.700	0.212	0.190	0.170	0.053	0.039	0.017
14	0.004	0.007	0.013	0.110	0.035	0.600	0.212	0.190	0.170	0.053	0.039	0.017
15	0.005	0.007	0.025	0.110	0.080	0.580	0.212	0.190	0.170	0.053	0.039	0.017
16	0.005	0.007	0.025	0.110	0.080	0.550	0.212	0.190	0.170	0.053	0.039	0.017
17	0.005	0.015	0.025	0.110	0.080	0.460	0.212	0.190	0.170	0.053	0.039	0.017
18	0.005	0.011	0.030	0.110	0.234	0.400	0.212	0.190	0.170	0.053	0.039	0.017
19	0.005	0.020	0.030	0.110	0.340	0.360	0.212	0.190	0.170	0.053	0.039	0.017
20	0.005	0.011	0.025	0.110	0.400	0.340	0.212	0.190	0.170	0.053	0.039	0.017
21	0.005	0.009	0.025	0.110	0.400	0.320	0.212	0.190	0.170	0.053	0.031	0.014
22	0.005	0.007	0.025	0.110	0.400	0.320	0.212	0.190	0.170	0.053	0.024	0.014
23	0.005	0.009	0.025	0.110	0.360	0.340	0.190	0.190	0.170	0.053	0.024	0.014
24	0.005	0.050	0.020	0.190	0.340	0.320	0.190	0.190	0.170	0.053	0.024	0.014
25	0.005	0.090	0.020	0.190	0.400	0.320	0.190	0.170	0.170	0.053	0.024	0.014
26	0.005	0.015	0.020	0.190	0.620	0.320	0.190	0.170	0.170	0.053	0.024	0.014
27	0.005	0.013	0.520	0.190	0.570	0.320	0.190	0.170	0.170	0.053	0.024	0.014
28	0.005	0.011	0.620	0.190	0.570	0.320	0.190	0.170	0.170	0.053	0.024	0.014
29	0.005	0.011	0.400	0.190	-----	0.300	0.190	0.170	0.170	0.053	0.024	0.014
30	0.005	0.009	0.380	0.150	-----	0.234	0.190	0.170	0.170	0.053	0.024	0.014
31	0.005	-----	0.700	0.080	-----	0.212	-----	0.170	-----	0.053	0.024	-----
Maks.	0.005	0.360	1.29	0.430	1.02	1.41	0.212	0.190	0.170	3.70	0.046	0.024
Min.	0.002	0.005	0.007	0.040	0.004	0.212	0.190	0.170	0.170	0.053	0.024	0.014
Ortalama	0.004	0.013	0.099	0.153	0.320	0.448	0.206	0.185	0.170	0.107	0.036	0.018
LT/SN/Km2	0.350	1.22	9.29	14.3	29.9	41.9	19.3	17.3	15.9	10.0	3.36	1.69
AKIM mm.	0.937	3.17	24.9	38.3	72.3	112.	49.9	46.4	41.2	26.9	9.00	4.38
MİL. M3	0.010	0.034	0.266	0.410	0.774	1.20	0.534	0.497	0.441	0.288	0.096	0.047

SU YILI (2006) YILLIK TOPLAM AKIM 4.60 MİLYON M3 430 MM. 13.6 LT/SN/Km2

02

MARMARA HAVZASI

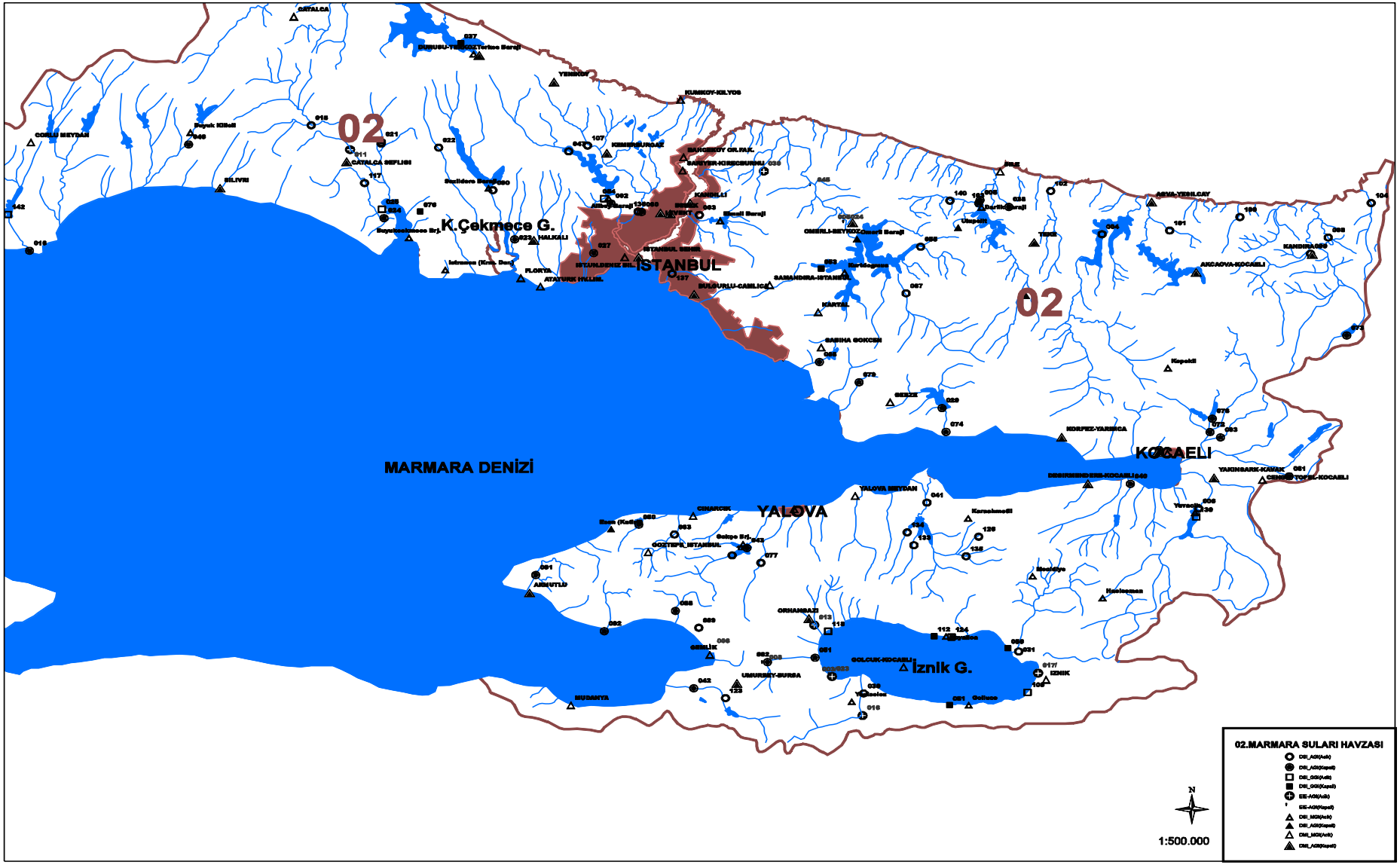
02.MARMARA SULARI HAVZASI
DSİ_AGİ(Aktif)
DSİ_AGİ(Kapalı)
DSİ_OGİ(Aktif)
DSİ_OGİ(Kapalı)
EE-KGİ(Aktif)
EE-KGİ(Kapalı)
DSİ_MGİ(Aktif)
DSİ_MGİ(Kapalı)
DMİ_AGİ(Aktif)
DMİ_AGİ(Kapalı)
N
1:500.000
MARMARA DENİZİ
İSTANBUL
K.Çekmece G.
İznik G.
KOCAELİ
YALOVA
02
02
ÇATALCA
SİLİVRİ
ATATÜRK HİLLİ.
FLORYA
SAMANDIRA-İSTANBUL
SULUURLU-CAMLICA
KARTAL
SARIHA SÖKÜCÜ
ÖMERLİ-BEYKOZ
YENİKOY
KUMKOY-KILYOS
SARIYER-KIREÇBURNU
KANDİLLİ
ASMA-YEŞİLÇAY
AKÇAOVA-KOCAELİ
KANDIRA-KOC
KORFEZ-YARIMCA
DİŞİRİŞİNDERE-KOCAELİ
YAKINBARK-KAHAK
YALOVA MEYDAN
Karaahmetli
Hacıköy
Hasbahçe
ORHANGAZI
GÖLCÜK-KOCAELİ
İZNİK
Gölcücü
UMURBEY-BURSA
GEMLİK
MUDANYA
ARMUTLU
GÖZTEPE_İSTANBUL
CINARCIK
Kapaklı
Yeniçağa

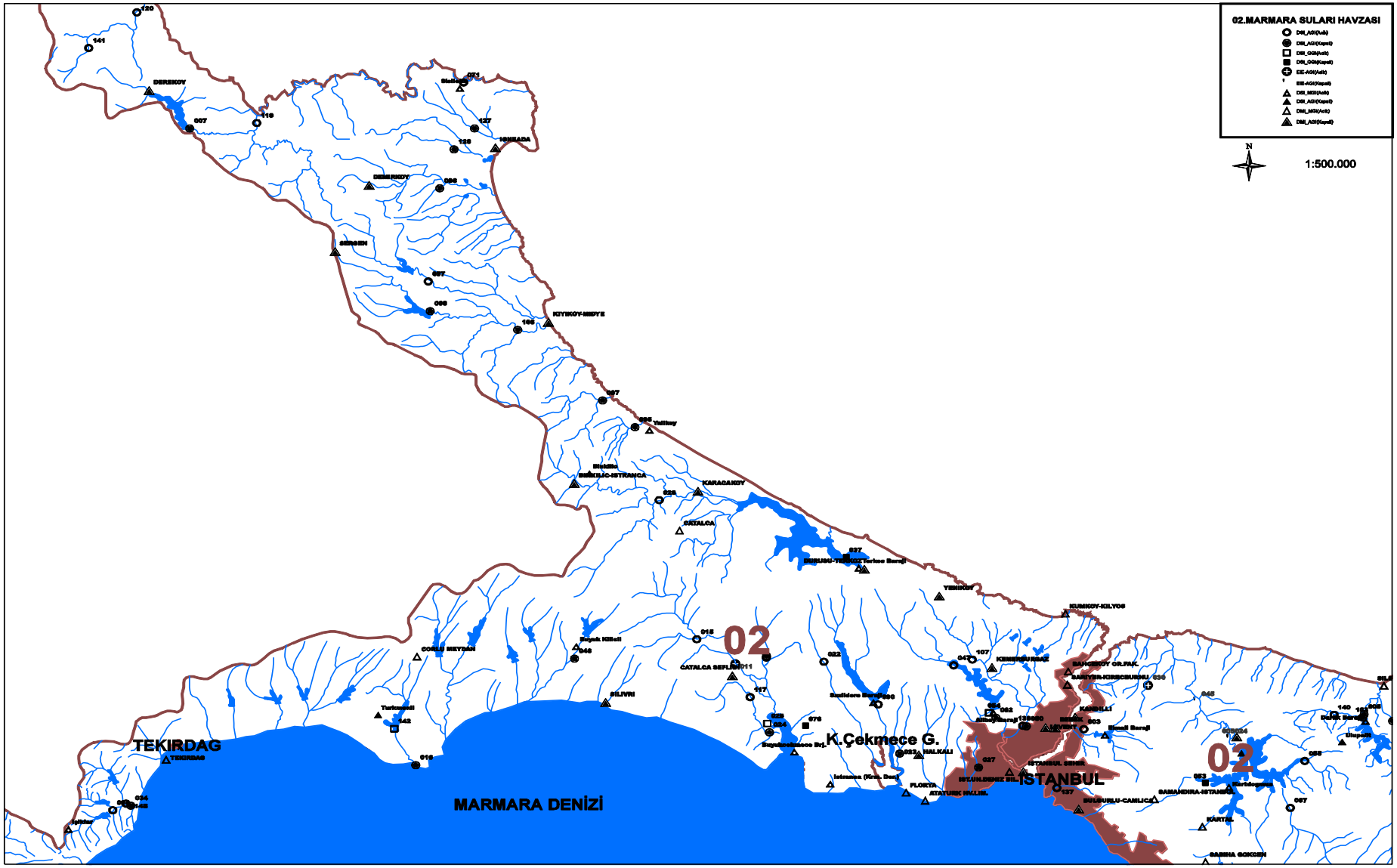
02.MARMARA SULARI HAVZASI
DSİ_AGİ(Aktif)
DSİ_AGİ(Kapalı)
DSİ_GGİ(Aktif)
DSİ_GGİ(Kapalı)
EE-AGİ(Aktif)
EE-AGİ(Kapalı)
DSİ_MGİ(Aktif)
DSİ_AGİ(Kapalı)
DSİ_MGİ(Aktif)
DSİ_AGİ(Kapalı)
N
1:500.000
02
02
TEKIRDAG
MARMARA DENİZİ
K.Çekmece G.
ISTANBUL
DERINKOY
IGNEADA
DEMIRKOY
SERGEN
KIYIKOY-MIDYE
Yeniköy
KARACAKOY
ÇATALCA
YENIKOY
KURNKOY-KILYOS
CORLU MEYDAN
SILIVRI
CATALCA SEFLIKKOY
HALKALI
FLORYA
ATATURK HVLIM.
BAHCESEHIR
KASIMLI
SAMANDIRA-ISTANBUL
KARTAL
SABIHA GOKCEN

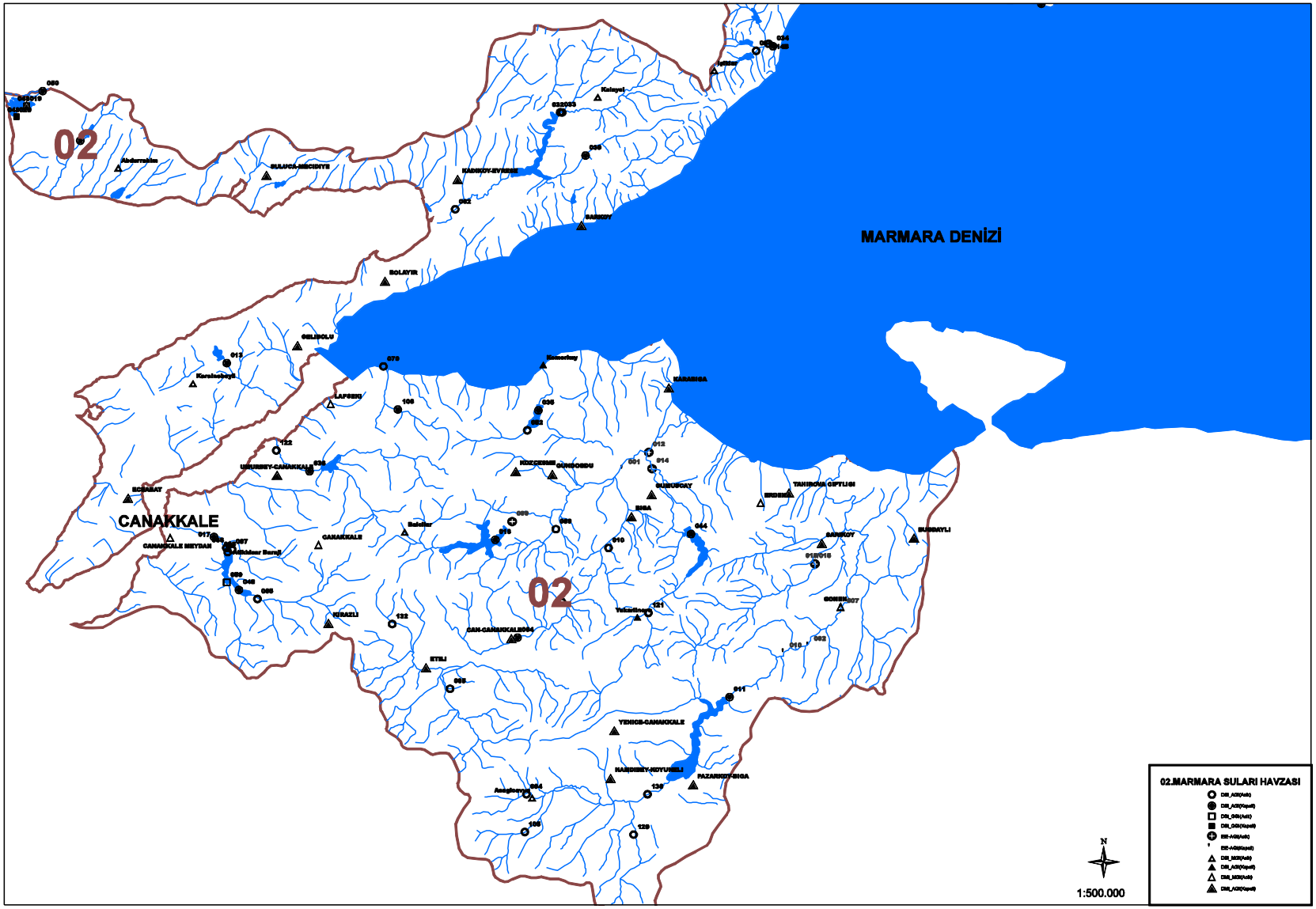
MARMARA DENİZİ
CANAKKALE
02
02
Kalaycı
Abdurrahim
SILAYCA-MECIDIYE
HAMIDIYE-EVRENE
BAHÇEKÖY
BOLAYIR
GELİBOLU
Karaağaçlı
LAPSEKI
HARMANCA
Kocaoğlay
ÜÇKUYU-CANAKKALE
BOZABAT
NEZİLİ-BAYRAM
GÜNÜGÖRDU
SUBUKÖY
TAHTACIK ÖPTLIGI
ERDEK
BIGA
Balıcılar
SARIKÖY
SUSURLU
CANAKKALE
CANAKKALE MEYDAN
Mehmet Barajı
YURAZLI
GÖNEN
YAZICILAR
CAN-CANAKKALE
ETELI
YENICE-CANAKKALE
HAMIDIYE-KOYUNELI
PAZARKEY-SIGA
Aşağıkaş
1:500.000
N
02.MARMARA SULARI HAVZASI

02. Marmara Havzasi

D02A004 GÖKSU D. GÖKSU

YERİ : **AĞVADAN ŞİLE İSTİKAMETİNE GİDEN KARAYOLUNUN 10. KM SİNDEKİ GÖKSÜ KÖYÜ SAPAĞINDAN SAPILARAK, 3 KM SONRA KÖY ÇIKIŞINDADIR. PAFTA 25.000: İST-F23-C4 29°46'34" Doğu - 41°4'36" Kuzey**

YAĞIŞ ALANI : **395,00 km2** **YAKLAŞIK KOT : 10 m**

GÖZLEM SÜRESİ : **20.08.1959 - 30.09.2006**

ORTALAMA AKIMLAR : **Gözlem süresinde 6.059 m3/sn. (45 Yıllık) 2006 Su yılında 8.211 m3/sn.**

ANLIK EN ÇOK VE EN AZ AKIMLAR:

2006 Su yılında anlık ençok akım	**:**	**188.**	**m3/sn**	**18.02.2006**
2006 Su yılında anlık enaz akım	**:**	**0.282**	**m3/sn**	**01.08.2006**
Gözlem süresinde anlık ençok akım	**:**	**588.**	**m3/sn**	**20.08.2001**
Gözlem süresinde anlık enaz akım	**:**	**0.000**	**m3/sn**	**08.08.1970**

10. Anahtar Eğrisi (Seviyeler cm olarak)

Seviye	Akım	Seviye	Akım	Seviye	Akım	Seviye	Akım
46	0.010	240	38.9	440	210.	640	554.
80	3.0	280	57.2	480	270.	680	638.
120	9.3	320	80.5	520	332.	720	726.
160	16.6	360	110.	560	398.	760	818.
200	25.9	400	150.	600	470.	800	910.

Akımlar 01 Ekim 2005 'den 30 Eylül 2006' a kadar m3/sn olarak

Gün	Ekim	Kasım	Aralık	Ocak	Şubat	Mart	Nisan	Mayıs	Haziran	Temmuz	Ağustos	Eylül
01	0.404	13.8	8.60	13.8	12.4	25.6	4.17	1.18	0.648	0.526	0.282	0.526
02	0.343	5.98	7.38	10.4	13.8	17.6	4.03	1.18	0.709	0.404	0.343	0.873
03	0.343	3.76	13.6	8.60	15.8	44.8	3.76	1.18	0.770	0.343	0.343	0.709
04	0.465	6.15	11.5	7.20	15.7	22.8	3.63	1.08	0.709	0.526	0.343	0.587
05	0.465	17.0	9.84	6.33	15.8	16.4	3.49	1.08	0.709	0.873	0.343	0.526
06	0.282	14.9	7.90	5.80	25.1	13.4	3.36	1.18	0.709	0.770	0.343	0.526
07	0.282	10.2	6.68	5.80	19.7	15.7	3.09	1.18	0.709	0.873	0.343	0.465
08	0.343	7.20	6.15	16.6	16.0	38.1	3.09	1.08	0.770	0.770	0.404	0.465
09	0.343	5.35	8.78	41.4	14.9	34.7	3.09	1.08	1.18	0.770	0.465	0.465
10	0.343	4.30	6.50	20.6	22.1	28.7	3.09	0.976	6.33	0.873	0.465	0.404
11	0.404	3.63	9.48	18.4	101.	34.7	2.84	0.976	1.80	1.18	0.465	0.404
12	0.404	3.09	10.4	20.1	35.8	45.8	2.72	0.873	0.873	0.976	0.465	0.404
13	0.404	4.45	8.60	25.4	23.1	21.8	2.61	0.976	0.770	0.648	0.465	0.404
14	0.404	13.1	7.03	33.0	18.2	17.4	2.38	0.976	1.59	0.587	0.465	0.404
15	1.29	17.2	6.15	17.8	15.8	18.6	2.38	0.770	1.18	0.526	0.404	0.343
16	7.03	10.9	6.68	13.3	14.2	14.5	2.15	0.709	0.770	0.526	0.465	0.343
17	3.36	7.55	12.4	10.9	17.8	13.3	2.15	0.709	0.648	0.587	0.465	0.343
18	1.70	7.38	14.2	9.30	90.9	12.0	2.03	0.648	0.526	0.587	0.526	0.343
19	0.976	11.6	51.8	18.2	83.8	11.3	1.92	0.648	0.526	0.587	0.526	0.343
20	0.709	29.6	21.6	28.1	82.5	10.2	1.80	0.873	0.587	0.465	0.465	0.526
21	0.648	67.6	14.7	17.0	64.8	9.30	1.80	0.873	0.587	0.465	0.404	0.404
22	0.526	17.6	11.6	15.8	55.7	8.43	1.70	0.770	0.587	0.465	0.404	0.465
23	0.465	12.4	11.8	14.9	44.4	7.20	1.59	0.770	0.526	0.465	0.404	0.976
24	0.404	21.6	12.2	14.0	32.4	6.85	1.59	0.770	0.770	0.465	0.404	1.29
25	0.343	15.7	11.6	13.6	27.9	6.68	1.49	0.648	0.770	0.465	0.404	5.35
26	0.343	21.6	13.8	12.9	44.8	6.15	1.39	0.648	0.873	0.404	0.404	2.61
27	0.343	13.8	16.4	12.4	32.4	5.65	1.29	0.648	0.873	0.404	0.404	0.587
28	0.343	11.5	14.9	11.6	21.3	5.05	1.29	0.648	0.873	0.404	0.404	0.343
29	0.404	11.3	17.8	10.9	-----	4.75	1.29	0.648	1.18	0.404	0.465	0.282
30	3.09	10.9	10.6	10.4	-----	4.60	1.29	0.648	0.873	0.404	0.465	0.282
31	17.6	-----	17.4	10.7	-----	4.45	-----	0.587	-----	0.404	0.465	-----
Maks.	KURU	127.	79.9	92.9	188.	107.	4.30	1.29	17.6	1.39	0.587	13.6
Min.	KURU	2.84	5.50	5.35	12.4	4.45	1.29	0.587	0.465	0.343	0.282	0.282
Ortalama	1.45	13.4	12.5	15.3	34.9	17.0	2.42	0.871	1.01	0.585	0.420	0.733
LT/SN/Km2	3.66	33.9	31.7	38.8	88.4	43.0	6.12	2.21	2.57	1.48	1.06	1.86
AKIM mm.	9.80	87.7	84.9	104.	214.	115.	15.9	5.91	6.65	3.97	2.85	4.81
MİL. M3	3.87	34.7	33.5	41.1	84.5	45.5	6.26	2.33	2.63	1.57	1.12	1.90

SU YILI (2006) YILLIK TOPLAM AKIM 258.98 MİLYON M3 656 MM. 20.8 LT/SN/Km2

02. Marmara Havzasi

D02A006 Kiraz D. YUVACIK

YERİ : **YALOVA-İZMİT KARAYOLUNUN YUVAÇIK YOL AYRIMINDAN SAĞA SAPILIR. YUVAÇIK BARAJINA DEVAM EDİLİR. AGİ BARAJIN 500M. MANSABINDAKİ KÖPRÜNÜN 15M. MANSABINDA VE SAĞ SAHİLDEDİR. 29°58'7" Doğu - 40°41'31" Kuzey**

YAĞIŞ ALANI : **257,97 km2** **YAKLAŞIK KOT : 37 m**

GÖZLEM SÜRESİ : **01.10.1963 - 30.09.2006**

ORTALAMA AKIMLAR : **Gözlem süresinde 5.100 m3/sn. (37 Yıllık) 2006 Su yılında 3.230 m3/sn.**

ANLIK EN ÇOK VE EN AZ AKIMLAR:

2006 Su yılında anlık ençok akım	:	47.9	m3/sn	03.03.2006
2006 Su yılında anlık enaz akım	:	0.010	m3/sn	05.10.2005
Gözlem süresinde anlık ençok akım	:	215.	m3/sn	14.11.1989
Gözlem süresinde anlık enaz akım	:	0.000	m3/sn	14.10.1988

13. Anahtar Eğrisi (Seviyeler cm olarak)

Seviye	Akım	Seviye	Akım	Seviye	Akım	Seviye	Akım
34	0.001	54	2.7	68	7.8	110	31.2
39	0.050	58	4.0	70	8.5	120	40.7
42	0.300	62	5.4	80	12.2	130	51.0
46	0.910	64	6.2	90	17.5	158	89.0
50	1.7	66	6.8	100	23.6	190	146.

Akımlar 01 Ekim 2005 'den 30 Eylül 2006' a kadar m3/sn olarak

Gün	Ekim	Kasım	Aralık	Ocak	Şubat	Mart	Nisan	Mayıs	Haziran	Temmuz	Ağustos	Eylül
01	0.200	0.050	0.200	15.4	1.70	31.2	0.100	0.100	0.100	0.300	0.100	0.200
02	0.200	0.050	0.200	4.00	2.25	28.2	0.200	0.050	0.300	0.300	0.100	0.200
03	0.050	0.050	0.200	0.200	2.49	35.0	0.100	0.050	0.300	0.300	0.100	0.200
04	0.050	0.050	0.200	0.200	2.73	36.9	0.100	0.100	0.200	0.300	0.100	0.200
05	0.010	0.050	0.200	0.200	3.35	24.4	0.200	0.100	0.200	0.300	0.100	0.100
06	0.010	0.050	0.200	6.20	3.68	19.9	0.300	0.100	0.200	0.300	0.100	0.100
07	0.010	0.050	0.200	16.4	4.00	19.9	0.300	0.200	0.200	0.100	0.100	0.100
08	0.010	0.050	0.200	9.24	3.35	23.0	0.420	0.200	0.200	0.200	0.100	0.100
09	0.010	0.050	0.200	7.30	3.04	21.2	0.420	0.300	0.300	0.200	0.050	0.100
10	0.010	0.050	0.100	5.78	3.04	16.4	0.420	0.300	0.300	0.200	0.050	0.050
11	0.010	0.050	0.100	4.65	14.9	15.4	0.420	0.300	0.300	0.200	0.050	0.050
12	0.010	0.050	0.200	4.00	14.3	29.7	0.420	0.300	0.200	0.200	0.050	0.050
13	0.010	0.050	0.100	5.35	10.4	35.0	0.540	0.300	0.300	0.200	0.050	0.100
14	0.010	0.050	0.100	6.20	7.80	29.7	0.540	0.300	0.300	0.200	0.050	0.100
15	0.010	0.100	0.200	5.78	6.20	29.7	0.540	0.300	0.300	0.200	0.050	0.100
16	0.050	0.050	0.200	4.00	4.65	22.4	0.420	0.100	0.300	0.200	0.050	0.100
17	0.050	0.050	0.300	3.35	4.00	18.1	0.300	0.100	0.300	0.200	0.050	0.100
18	0.050	0.050	0.300	2.73	6.80	15.4	0.300	0.100	0.300	0.200	0.050	0.100
19	0.050	0.050	0.725	3.35	14.9	13.8	0.300	0.100	0.300	0.200	0.050	0.100
20	0.050	0.100	0.540	8.15	21.8	12.2	0.300	0.200	0.300	0.200	0.050	0.100
21	0.010	0.300	0.420	6.80	23.0	11.5	0.300	0.300	0.300	0.200	0.050	0.100
22	0.050	0.100	0.420	5.35	23.6	11.8	0.300	0.100	0.300	0.200	0.100	0.100
23	0.050	0.050	0.420	5.00	23.6	14.9	0.300	0.100	0.200	0.100	0.200	0.100
24	0.050	0.050	0.420	5.00	23.6	18.1	0.200	0.100	0.200	0.100	0.200	0.200
25	0.050	0.050	0.300	4.00	25.9	16.4	0.200	0.050	0.200	0.100	0.200	0.200
26	0.050	0.200	0.420	3.68	35.0	13.3	0.200	0.050	0.200	0.100	0.200	0.100
27	0.050	0.300	0.540	3.04	35.0	10.7	0.200	0.050	0.200	0.100	0.200	0.050
28	0.050	0.300	0.540	2.49	23.0	10.4	0.100	0.050	0.300	0.100	0.200	0.050
29	0.050	0.300	0.540	2.25	-----	9.98	0.100	0.050	0.420	0.100	0.200	0.050
30	0.050	0.300	8.50	1.70	-----	5.00	0.100	0.100	0.420	0.100	0.200	0.050
31	0.050	-----	22.4	1.70	-----	0.100	-----	0.100	-----	0.100	0.200	-----
Maks.	0.420	0.540	30.4	23.0	41.7	47.9	0.540	0.300	0.420	0.420	0.200	0.200
Min.	0.010	0.050	0.100	0.200	0.725	0.100	0.100	0.050	0.100	0.100	0.050	0.050
Ortalama	0.044	0.102	1.28	4.95	12.4	19.3	0.288	0.150	0.265	0.187	0.108	0.108
LT/SN/Km2	0.171	0.394	4.95	19.2	48.2	75.0	1.12	0.581	1.03	0.725	0.419	0.420
AKIM mm.	0.459	1.02	13.3	51.4	117.	201.	2.89	1.56	2.66	1.94	1.12	1.09
MİL. M3	0.118	0.264	3.42	13.3	30.1	51.8	0.746	0.402	0.686	0.501	0.289	0.281

SU YILI (2006) YILLIK TOPLAM AKIM 101.91 MİLYON M3 395 MM. 12.5 LT/SN/Km2

02. Marmara Havzasi

D02A010 Kocabaş Çayı Akkayrak

YERİ : **1981 BİGA - ÇAN KARAYOLUNUN 7.KM.SINDEKI AKKAYRAK KÖYÜ KÖPRÜSÜNDEDIR.**
27°12'46" Doğu - 40°10'14" Kuzey

YAĞIŞ ALANI : **975.80 km2** **YAKLAŞIK KOT : 29 m**

GÖZLEM SÜRESİ : **08.12.1964 - 30.09.2006**

ORTALAMA AKIMLAR : **Gözlem süresinde 7.641 m3/sn. (38 Yıllık) 2006 Su yılında 7.036 m3/sn.**

ANLIK EN ÇOK VE EN AZ AKIMLAR:

2006 Su yılında anlık ençok akım	**:**	**131.**	**m3/sn**	**08.03.2006**
2006 Su yılında anlık enaz akım	**:**	**0.101**	**m3/sn**	**08.08.2006**
Gözlem süresinde anlık ençok akım	**:**	**960.**	**m3/sn**	**03.03.1971**
Gözlem süresinde anlık enaz akım	**:**	**0.000**	**m3/sn**	**10.10.1981**

26. Anahtar Eğrisi (Seviyeler cm olarak)

Seviye	Akım	Seviye	Akım	Seviye	Akım	Seviye	Akım
7	0.020	181	52.0	286	90.0	484	200.
36	3.6	202	61.0	307	98.0	505	230.
100	23.0	223	68.0	328	105.	526	250.
139	38.0	244	75.0	389	130.	547	300.
160	45.0	265	83.0	463	180.	568	360.

Akımlar 01 Ekim 2005 'den 30 Eylül 2006' a kadar m3/sn olarak

Gün	Ekim	Kasım	Aralık	Ocak	Şubat	Mart	Nisan	Mayıs	Haziran	Temmuz	Ağustos	Eylül
01	0.195	0.385	2.05	7.88	5.31	3.54	10.8	3.25	0.692	0.783	0.172	0.338
02	0.243	0.433	1.69	5.02	7.48	3.54	9.85	3.25	0.783	0.783	0.172	0.338
03	0.338	0.433	1.51	3.54	14.8	4.13	9.06	2.77	1.87	1.15	0.172	0.338
04	0.290	0.433	1.51	2.95	50.2	24.4	8.67	2.59	1.87	1.15	0.172	0.338
05	0.290	0.385	1.33	2.41	68.0	17.2	8.27	2.41	1.87	0.967	0.172	0.290
06	0.243	0.385	1.33	2.23	66.4	14.3	7.88	2.23	1.87	0.875	0.172	0.290
07	0.243	0.385	1.15	2.05	48.5	14.8	7.48	2.05	1.87	0.875	0.172	0.290
08	0.243	0.385	1.15	1.87	22.9	114.	7.48	1.87	1.87	0.875	0.148	0.290
09	0.195	0.433	1.06	1.69	17.8	61.1	7.48	1.51	2.59	0.692	0.172	0.290
10	0.195	0.385	0.967	1.51	52.0	39.0	7.09	1.15	2.95	0.692	0.148	0.290
11	0.480	0.385	0.967	1.69	66.4	33.8	6.69	1.87	2.77	0.600	0.148	0.290
12	1.33	0.385	0.967	2.77	80.0	35.5	6.69	2.41	2.59	0.600	0.148	0.290
13	0.600	0.385	0.967	6.30	74.8	39.6	6.30	2.95	2.41	0.540	0.148	0.290
14	0.480	0.433	0.967	7.88	56.1	39.6	5.90	3.25	2.41	0.480	0.148	0.290
15	0.433	0.433	0.967	7.09	20.7	39.0	5.90	2.59	2.41	0.385	0.148	0.338
16	0.433	0.385	0.875	7.09	12.3	36.7	5.61	2.41	3.54	0.338	0.172	0.290
17	0.385	0.433	0.875	7.09	6.69	34.4	5.31	2.05	2.77	0.290	0.148	0.290
18	0.385	0.480	7.09	6.30	5.31	30.3	5.31	2.05	2.41	0.290	0.148	0.290
19	0.385	0.600	16.0	10.8	4.43	56.5	5.02	1.87	2.23	0.290	0.148	0.290
20	0.385	0.692	12.3	16.6	4.43	39.0	5.02	1.69	2.05	0.243	0.125	0.290
21	0.385	0.967	5.61	10.3	3.84	30.9	5.02	1.51	1.87	0.243	0.148	0.243
22	0.338	0.875	3.84	6.69	11.8	25.8	5.02	1.33	1.69	0.195	0.172	0.243
23	0.338	0.875	2.95	7.88	15.4	21.4	4.72	1.15	1.69	0.243	0.243	0.243
24	0.338	1.51	2.41	11.3	59.9	19.5	4.43	1.15	1.51	0.338	0.243	0.290
25	0.338	7.88	2.05	7.09	80.0	20.1	4.13	1.06	1.51	0.540	0.195	0.480
26	0.385	29.7	1.87	5.02	67.2	17.8	4.13	0.967	1.33	0.480	0.195	0.600
27	0.385	10.3	1.69	5.02	48.0	16.0	3.84	0.967	1.33	0.338	0.195	0.600
28	0.385	5.31	1.69	4.43	36.1	14.3	3.54	0.875	1.15	0.385	0.195	0.540
29	0.385	3.54	1.69	3.54	-----	13.3	3.84	0.875	0.783	0.290	0.243	0.692
30	0.385	2.59	2.77	3.54	-----	12.3	3.54	0.875	0.783	0.195	0.243	0.967
31	0.385	-----	5.61	4.13	-----	11.8	-----	0.783	-----	0.172	0.338	-----
Maks.	2.23	43.1	46.7	35.5	80.0	131.	11.3	4.43	4.43	1.15	0.338	1.06
Min.	0.195	0.338	0.875	1.51	3.84	3.25	2.05	0.385	0.480	0.172	0.101	0.243
Ortalama	0.381	2.41	2.84	5.60	36.0	28.5	6.13	1.86	1.92	0.526	0.179	0.365
LT/SN/Km2	0.391	2.47	2.91	5.74	36.8	29.2	6.29	1.91	1.96	0.539	0.184	0.374
AKIM mm.	1.05	6.39	7.78	15.4	89.1	78.2	16.3	5.11	5.09	1.44	0.493	0.968
MİL. M3	1.02	6.24	7.59	15.0	87.0	76.3	15.9	4.99	4.97	1.41	0.481	0.945

SU YILI (2006) YILLIK TOPLAM AKIM 221.85 MİLYON M3 227 MM. 7.2 LT/SN/Km2

02. Marmara Havzasi

D02A015 KARASU D. İNCEĞİZ

YERİ : **ÇATALCADAN İNCEĞİZ KÖYÜ İSTİKAMETİNE DOĞRU GİDİLİR. KÖY GİRİŞİNDEKİ KARAYOLU KÖPRÜSÜ ÜZERİDEDİR. PAFTA 25.000:KIRK-F20-B1**
28°24'40" Doğu - 41°11'14" Kuzey

YAĞIŞ ALANI : **174,90 km2** **YAKLAŞIK KOT : 30 m**

GÖZLEM SÜRESİ : **16.09.1965 - 30.09.2006**

ORTALAMA AKIMLAR : **Gözlem süresinde 0.999 m3/sn. (38 Yıllık) 2006 Su yılında 2.466 m3/sn.**

ANLIK EN ÇOK VE EN AZ AKIMLAR:

2006 Su yılında anlık ençok akım	**:**	**164.**	**m3/sn**	**18.12.2005**
2006 Su yılında anlık enaz akım	**:**	**0.031**	**m3/sn**	**24.08.2006**
Gözlem süresinde anlık ençok akım	**:**	**350.**	**m3/sn**	**15.01.1981**
Gözlem süresinde anlık enaz akım	**:**	**0.000**	**m3/sn**	**09.08.1968**

15. Anahtar Eğrisi (Seviyeler cm olarak)

Seviye	Akım	Seviye	Akım	Seviye	Akım	Seviye	Akım
110	0.001	250	10.0	400	54.0	550	156.
130	0.270	280	15.7	430	69.0	580	185.
160	1.7	310	22.4	460	85.0	590	196.
190	3.8	340	31.0	490	107.	600	207.
220	6.4	370	42.0	520	131.		

Akımlar 01 Ekim 2005 'den 30 Eylül 2006' a kadar m3/sn olarak

Gün	Ekim	Kasım	Aralık	Ocak	Şubat	Mart	Nisan	Mayıs	Haziran	Temmuz	Ağustos	Eylül
01	0.081	0.274	0.418	3.32	5.90	4.12	1.76	0.612	0.250	0.151	0.061	0.091
02	0.107	0.210	0.418	1.82	7.81	5.03	1.59	0.612	0.230	0.151	0.091	0.111
03	0.107	0.210	4.20	1.54	5.90	8.65	1.54	0.574	0.230	0.171	0.111	0.091
04	0.081	0.242	1.50	1.48	5.63	3.16	1.48	0.574	0.210	0.171	0.061	0.071
05	0.081	0.184	0.940	1.32	9.55	2.37	1.37	0.574	0.210	0.151	0.061	0.061
06	0.081	0.184	0.802	1.32	7.93	2.06	1.32	0.574	0.210	0.131	0.051	0.061
07	0.081	0.158	0.706	1.21	4.86	24.3	1.26	0.574	0.210	0.111	0.051	0.051
08	0.070	0.158	0.658	1.21	4.86	17.4	1.37	0.700	0.210	0.111	0.151	0.051
09	0.070	0.158	0.850	1.21	4.20	11.3	1.26	0.850	0.250	0.111	0.131	0.051
10	0.070	0.158	0.706	7.47	34.4	6.95	1.15	0.612	0.346	0.111	0.071	0.051
11	0.081	0.158	0.610	33.1	30.1	5.90	1.15	0.574	0.250	0.131	0.071	0.051
12	0.107	0.158	0.610	39.6	13.3	5.11	1.10	0.574	0.250	0.111	0.061	0.061
13	0.081	0.158	0.610	19.1	7.58	3.88	1.05	0.574	0.250	0.111	0.061	0.061
14	0.081	0.210	0.562	8.80	8.16	14.1	1.05	0.536	0.270	0.111	0.051	0.061
15	0.107	0.242	0.562	4.04	5.20	6.65	1.00	0.498	0.384	0.111	0.061	0.061
16	0.210	0.184	0.610	3.24	3.80	11.3	0.950	0.460	0.422	0.091	0.071	0.061
17	0.158	0.210	1.17	2.30	3.16	4.52	0.900	0.422	0.270	0.091	0.061	0.061
18	0.107	0.242	30.4	1.94	26.0	2.93	0.850	0.422	0.250	0.190	0.061	0.061
19	0.107	0.274	39.2	5.28	32.2	2.30	0.800	0.384	0.230	0.131	0.071	0.091
20	0.107	0.562	5.99	8.16	18.5	2.00	0.800	0.384	0.210	0.111	0.071	0.071
21	0.107	1.17	2.51	2.65	19.1	1.82	0.750	0.346	0.210	0.091	0.061	0.071
22	0.107	0.370	2.00	2.06	11.4	1.76	0.700	0.346	0.210	0.071	0.051	0.111
23	0.081	0.274	1.70	1.88	8.50	1.70	0.700	0.346	0.190	0.061	0.041	0.250
24	0.081	1.75	1.48	1.59	5.99	12.6	0.700	0.308	0.190	0.061	0.041	0.171
25	0.081	3.29	1.32	1.65	7.25	3.00	0.650	0.308	0.171	0.061	0.061	1.65
26	0.107	6.26	1.37	1.65	12.4	2.00	0.612	0.308	0.171	0.071	0.061	0.270
27	0.107	1.17	2.37	1.76	24.6	1.76	0.612	0.270	0.171	0.071	0.051	0.210
28	0.107	0.754	3.80	1.82	13.3	1.65	0.612	0.270	0.171	0.071	0.061	0.190
29	0.107	0.562	2.06	1.70	-----	1.54	0.650	0.270	0.171	0.061	0.111	0.190
30	0.466	0.466	1.65	1.70	-----	6.95	0.700	0.270	0.151	0.061	0.071	0.190
31	0.940	-----	11.4	2.00	-----	2.24	-----	0.250	-----	0.061	0.061	-----
Maks.	1.80	20.2	164.	44.4	58.5	46.4	1.88	0.900	0.650	0.230	0.460	4.86
Min.	0.070	0.158	0.370	1.15	2.93	1.54	0.612	0.250	0.131	0.051	0.031	0.051
Ortalama	0.138	0.680	3.97	5.42	12.2	5.84	1.01	0.464	0.232	0.106	0.069	0.154
LT/SN/Km2	0.787	3.89	22.7	31.0	69.8	33.4	5.80	2.65	1.32	0.609	0.397	0.883
AKIM mm.	2.11	10.1	60.9	83.0	169.	89.4	15.0	7.10	3.43	1.63	1.06	2.29
MİL. M3	0.369	1.76	10.6	14.5	29.5	15.6	2.63	1.24	0.600	0.285	0.186	0.400

SU YILI (2006) YILLIK TOPLAM AKIM 77.67 MİLYON M3 444 MM. 14.1 LT/SN/Km2

02. Marmara Havzasi

D02A028 ISTIRANCA D. KARAMANDERE

YERİ : **ÇATALCA - KARACAKÖY BUCAĞI YOLUNUN 23. KM SİNDEKİ KARAMANDERE KÖYÜNÜN 1 KM MANSABINDADIR**
PAFTA 25.000: KIRK-F20-B1
28°18'44" Doğu - 41°22'45" Kuzey

YAĞIŞ ALANI : **287,10 km2** **YAKLAŞIK KOT : 32 m**

GÖZLEM SÜRESİ : **01.07.1966 - 30.09.2006**

ORTALAMA AKIMLAR : **Gözlem süresinde 2.402 m3/sn. (40 Yıllık) 2006 Su yılında 4.605 m3/sn.**

ANLIK EN ÇOK VE EN AZ AKIMLAR:

2006 Su yılında anlık ençok akım	**:**	**226.**	**m3/sn**	**02.07.2006**
2006 Su yılında anlık enaz akım	**:**	**0.188**	**m3/sn**	**15.09.2006**
Gözlem süresinde anlık ençok akım	**:**	**380.**	**m3/sn**	**05.10.1973**
Gözlem süresinde anlık enaz akım	**:**	**0.000**	**m3/sn**	**30.06.1990**

13. Anahtar Eğrisi (Seviyeler cm olarak)

Seviye	Akım	Seviye	Akım	Seviye	Akım	Seviye	Akım
1	0.002	80	4.6	280	106.	480	281.
10	0.030	120	14.4	320	141.	490	291.
14	0.060	160	31.5	360	171.	500	301.
18	0.110	200	52.6	400	211.	510	311.
40	0.800	240	78.6	440	241.	520	321.

Akımlar 01 Ekim 2005 'den 30 Eylül 2006' a kadar m3/sn olarak

Gün	Ekim	Kasım	Aralık	Ocak	Şubat	Mart	Nisan	Mayıs	Haziran	Temmuz	Ağustos	Eylül
01	0.332	1.10	1.28	7.45	4.65	18.8	3.40	1.16	0.422	0.422	0.308	0.284
02	0.356	0.716	1.16	4.03	8.08	9.90	3.06	1.10	0.422	16.0	0.308	0.308
03	0.356	0.590	1.91	3.06	10.2	20.4	2.83	1.04	0.464	24.9	0.308	0.308
04	0.356	1.16	1.66	2.60	9.06	9.62	2.60	1.04	0.422	2.94	0.308	0.284
05	0.332	0.716	1.28	2.25	9.62	6.82	2.48	0.920	0.356	1.57	0.284	0.260
06	0.308	0.590	1.10	2.37	16.0	5.35	2.25	0.980	0.380	1.22	0.284	0.260
07	0.284	0.548	1.04	3.53	8.78	13.2	2.17	1.04	0.422	0.980	0.284	0.236
08	0.284	0.506	0.980	3.65	8.08	34.9	2.25	0.980	0.422	1.10	0.356	0.236
09	0.284	0.464	1.74	2.83	6.82	17.2	2.17	1.28	102.	0.716	0.332	0.236
10	0.284	0.422	1.16	3.40	13.2	17.2	2.00	1.04	11.0	0.674	0.332	0.236
11	0.260	0.380	1.04	7.45	33.5	25.7	2.00	1.04	3.29	0.674	0.308	0.236
12	0.284	0.380	0.980	36.8	21.6	21.6	1.91	1.04	1.91	0.632	0.284	0.236
13	0.308	0.548	0.920	34.0	12.9	13.5	1.83	0.920	1.34	0.590	0.284	0.236
14	0.308	1.16	0.920	12.5	9.62	17.2	1.74	0.860	1.28	0.590	0.284	0.236
15	0.284	1.57	0.860	11.0	7.03	21.6	1.66	0.800	3.17	0.548	0.260	0.212
16	0.506	0.980	0.980	11.9	5.70	13.2	1.57	0.800	2.08	0.506	0.260	0.188
17	0.674	0.758	1.83	8.29	13.5	11.0	1.57	0.758	1.22	0.464	0.236	0.212
18	0.422	0.758	26.1	7.03	51.6	7.66	1.49	0.758	0.980	0.464	0.236	0.212
19	0.332	1.10	36.8	13.5	43.4	6.23	1.49	0.758	0.860	0.422	0.236	0.212
20	0.308	3.40	9.62	17.2	45.5	5.18	1.40	0.716	0.758	0.464	0.236	0.260
21	0.308	3.17	4.83	8.29	33.0	4.53	1.34	0.674	0.716	0.422	0.236	0.464
22	0.308	1.66	3.65	7.24	26.1	4.03	1.34	0.632	0.674	0.380	0.236	0.716
23	0.284	1.28	3.06	6.23	22.0	3.78	1.28	0.632	0.632	0.380	0.236	0.800
24	0.284	9.62	2.48	5.00	19.6	8.08	1.28	0.590	0.590	0.356	0.236	2.08
25	0.284	14.1	2.17	4.53	27.5	8.50	1.28	0.590	0.590	0.356	0.236	21.6
26	0.308	12.9	2.17	4.15	25.3	5.00	1.22	0.590	0.548	0.356	0.236	1.40
27	0.308	3.90	7.24	3.78	21.2	4.15	1.16	0.590	0.506	0.356	0.236	0.758
28	0.308	2.60	13.2	3.40	12.2	3.65	1.16	0.548	0.506	0.332	0.236	0.674
29	0.332	1.91	5.70	3.17	-----	3.40	1.16	0.548	0.464	0.332	0.308	0.632
30	0.590	1.49	3.53	3.17	-----	3.53	1.22	0.506	0.422	0.332	0.332	0.716
31	2.83	-----	11.9	3.78	-----	4.15	-----	0.464	-----	0.308	0.308	-----
Maks.	7.03	36.8	113.	62.2	81.0	48.0	3.78	1.49	204.	226.	0.674	178.
Min.	0.260	0.380	0.860	2.17	4.40	3.29	1.16	0.464	0.356	0.308	0.236	0.188
Ortalama	0.420	2.35	4.94	7.99	18.8	11.3	1.81	0.819	4.63	1.93	0.276	1.16
LT/SN/Km2	1.46	8.18	17.2	27.8	65.4	39.2	6.31	2.85	16.1	6.72	0.962	4.03
AKIM mm.	3.91	21.2	46.1	74.5	158.	105.	16.3	7.64	41.8	18.0	2.58	10.5
MİL. M3	1.12	6.09	13.2	21.4	45.4	30.2	4.69	2.19	12.0	5.17	0.740	3.00

SU YILI (2006) YILLIK TOPLAM AKIM 145.20 MİLYON M3 506 MM. 16.0 LT/SN/Km2

02. Marmara Havzasi

D02A030 Kocadere SÖLÖZ

YERİ : **GEMLİK-İZNİK YOLU TAKİP EDİLEREK SÖLÖZ BELDESİNE GELİNİR. AGİ BELDENİN ÇIKIŞINDA BULKUNAN KOCADERENİN ÜZERİNDEKİ KARAYOLU KÖPRÜSÜNÜN 3M. MENBAINDADIR. 29°25'0" Doğu - 40°2'4" Kuzey**

YAĞIŞ ALANI : **76,90 km2** **YAKLAŞIK KOT : 98 m**

GÖZLEM SÜRESİ : **06.09.1966 -30.09.2006**

ORTALAMA AKIMLAR : **Gözlem süresinde 0.769 m3/sn. (40 Yıllık) 2006 Su yılında 1.051 m3/sn.**

ANLIK EN ÇOK VE EN AZ AKIMLAR:

2006 Su yılında anlık ençok akım	**:**	**30.8**	**m3/sn**	**11.02.2006**
2006 Su yılında anlık enaz akım	**:**	**0.001**	**m3/sn**	**21.09.2006**
Gözlem süresinde anlık ençok akım	**:**	**110.**	**m3/sn**	**24.04.1969**
Gözlem süresinde anlık enaz akım	**:**	**0.000**	**m3/sn**	**16.07.1968**

13. Anahtar Eğrisi (Seviyeler cm olarak)

Seviye	Akım	Seviye	Akım	Seviye	Akım	Seviye	Akım
6	0.000	16	0.175	30	1.8	130	42.4
8	0.000	18	0.310	50	6.4	150	55.2
10	0.005	20	0.470	70	13.3	170	70.2
12	0.025	22	0.670	90	21.5	190	86.3
14	0.077	24	0.890	110	31.3	200	94.7

Akımlar 01 Ekim 2005 'den 30 Eylül 2006' a kadar m3/sn olarak

Gün	Ekim	Kasım	Aralık	Ocak	Şubat	Mart	Nisan	Mayıs	Haziran	Temmuz	Ağustos	Eylül
01	0.025	0.245	0.560	3.56	1.18	7.27	1.18	0.470	0.175	0.245	0.077	0.025
02	0.025	0.175	0.470	2.02	1.80	6.16	1.18	0.470	0.175	0.175	0.077	0.025
03	0.077	0.120	0.670	1.34	2.02	12.1	1.03	0.470	0.175	0.175	0.077	0.025
04	0.045	0.175	0.560	1.03	2.46	5.20	1.03	0.470	0.175	0.175	0.077	0.025
05	0.025	0.175	0.470	0.890	2.46	4.24	1.18	0.470	0.175	0.175	0.077	0.025
06	0.025	0.175	0.395	0.890	2.24	4.00	1.18	0.470	0.175	0.175	0.077	0.025
07	0.025	0.245	0.395	0.890	1.49	3.78	1.03	0.470	0.175	0.175	0.045	0.025
08	0.025	0.245	0.395	1.03	1.49	3.78	0.890	0.470	0.175	0.175	0.025	0.012
09	0.025	0.175	0.395	1.49	1.34	3.78	0.890	0.470	0.245	0.175	0.025	0.012
10	0.025	0.175	0.395	1.34	3.34	3.34	0.890	0.470	0.245	0.175	0.025	0.012
11	0.025	0.175	0.395	1.18	19.8	5.68	0.890	0.470	0.245	0.175	0.025	0.012
12	0.045	0.175	0.395	0.890	5.92	8.43	0.890	0.470	0.175	0.175	0.025	0.012
13	0.045	0.175	0.310	0.890	4.00	4.96	0.890	0.470	0.245	0.175	0.025	0.012
14	0.045	0.175	0.310	0.890	3.12	4.00	0.890	0.470	0.310	0.175	0.025	0.005
15	0.045	0.310	0.310	0.890	2.24	3.78	0.780	0.470	0.310	0.175	0.025	0.005
16	0.045	0.245	0.560	0.780	1.80	3.56	0.780	0.395	0.310	0.175	0.025	0.005
17	0.175	0.245	1.03	0.670	1.65	3.12	0.780	0.395	0.310	0.175	0.025	0.005
18	0.175	0.310	0.670	0.670	2.24	2.90	0.780	0.395	0.245	0.175	0.025	0.005
19	0.120	0.310	0.890	1.80	4.72	2.68	0.780	0.395	0.245	0.175	0.025	0.005
20	0.120	0.780	0.780	2.68	6.98	2.46	0.670	0.395	0.245	0.175	0.025	0.005
21	0.120	0.670	0.780	1.65	6.69	2.24	0.670	0.395	0.245	0.175	0.025	0.001
22	0.120	0.395	0.670	1.49	6.69	2.02	0.670	0.395	0.245	0.175	0.025	0.001
23	0.120	0.395	0.670	1.49	6.40	2.02	0.670	0.395	0.245	0.175	0.025	0.001
24	0.120	0.470	0.560	1.34	6.69	1.80	0.560	0.395	0.245	0.175	0.025	0.001
25	0.120	1.18	0.560	1.34	6.98	1.65	0.560	0.310	0.245	0.120	0.025	0.001
26	0.120	1.65	0.560	1.18	10.9	1.65	0.560	0.310	0.245	0.077	0.025	0.001
27	0.120	1.49	0.670	1.18	9.70	1.49	0.470	0.310	0.245	0.077	0.025	0.001
28	0.175	0.890	2.46	1.18	6.69	1.49	0.470	0.310	0.245	0.077	0.025	0.001
29	0.245	0.780	3.56	1.18	-----	1.49	0.470	0.310	0.245	0.077	0.025	0.001
30	0.175	0.670	2.02	1.18	-----	1.34	0.560	0.310	0.245	0.077	0.025	0.001
31	0.310	-----	7.56	1.03	-----	1.34	-----	0.245	-----	0.077	0.025	-----
Maks.	0.890	4.96	10.9	5.92	30.8	19.8	1.18	0.670	0.310	0.245	0.077	0.025
Min.	0.025	0.120	0.245	0.560	1.18	1.18	0.470	0.175	0.175	0.045	0.025	0.001
Ortalama	0.094	0.446	0.981	1.29	4.75	3.67	0.809	0.410	0.233	0.157	0.036	0.010
LT/SN/Km2	1.22	5.81	12.8	16.8	61.8	47.7	10.5	5.33	3.03	2.04	0.464	0.127
AKIM mm.	3.27	15.0	34.2	45.0	149.	128.	27.3	14.3	7.84	5.45	1.24	0.328
MİL. M3	0.251	1.16	2.63	3.46	11.5	9.83	2.10	1.10	0.603	0.419	0.096	0.025

SU YILI (2006) YILLIK TOPLAM AKIM 33.17 MİLYON M3 431 MM. 13.7 LT/SN/Km2

02. Marmara Havzasi

D02A031 Karadere ÇAKIRCA

YERİ : **İZNİK BOYALICA KARAYOLUNUN 10.KM.SİNDEKİ KARADERE KARAYOLU KÖPRÜSÜNÜN 200M. MANSABINDA VE SOL SAHİLDEDİR.**
29°41'7" Doğu - 40°28'5" Kuzey

YAĞIŞ ALANI : **234,00 km2** **YAKLAŞIK KOT : 11 m**

GÖZLEM SÜRESİ : **06.09.1966 - 30.09.2006**

ORTALAMA AKIMLAR : **Gözlem süresinde 2.172 m3/sn. (33 Yıllık) 2006 Su yılında 2.744 m3/sn.**

ANLIK EN ÇOK VE EN AZ AKIMLAR:

2006 Su yılında anlık ençok akım	:	74.0	m3/sn	11.02.2006
2006 Su yılında anlık enaz akım	:	0.010	m3/sn	08.09.2006
Gözlem süresinde anlık ençok akım	:	270.	m3/sn	18.10.1989
Gözlem süresinde anlık enaz akım	:	0.000	m3/sn	01.10.1970

15. Anahtar Eğrisi (Seviyeler cm olarak)

Seviye	Akım	Seviye	Akım	Seviye	Akım	Seviye	Akım
1	0.000	30	3.6	99	45.3	146	95.0
6	0.026	46	9.3	120	66.0	150	100.
10	0.240	66	20.0	133	80.0	160	115.
14	0.620	91	39.3	137	84.0	192	157.
19	1.3	95	42.3	142	90.0	268	270.

Akımlar 01 Ekim 2005 'den 30 Eylül 2006' a kadar m3/sn olarak

Gün	Ekim	Kasım	Aralık	Ocak	Şubat	Mart	Nisan	Mayıs	Haziran	Temmuz	Ağustos	Eylül
01	0.620	1.47	0.740	9.30	3.10	18.8	2.63	1.80	0.740	0.740	0.240	0.026
02	0.620	0.980	0.620	5.72	4.42	15.3	2.63	1.63	0.740	0.740	0.240	0.026
03	2.20	0.980	0.520	4.42	4.71	25.3	2.63	1.47	0.620	0.620	0.240	0.026
04	0.740	1.30	0.520	3.33	5.36	12.0	3.55	1.47	0.740	0.620	0.160	0.026
05	0.520	3.10	0.420	3.10	5.36	6.44	3.55	1.47	0.620	0.620	0.160	0.026
06	0.420	2.63	0.240	2.87	5.00	5.36	3.33	1.47	0.520	0.520	0.160	0.026
07	0.420	3.55	0.240	2.63	3.55	6.08	3.10	1.47	0.620	0.420	0.100	0.026
08	0.320	2.40	0.160	2.40	3.55	6.44	3.10	1.47	0.860	0.320	0.100	0.010
09	0.240	1.63	0.240	2.63	3.33	4.42	2.87	1.47	0.980	0.420	0.100	0.026
10	0.320	1.30	0.160	2.40	6.80	8.03	2.87	1.47	1.14	0.240	0.100	0.026
11	0.240	1.14	0.320	2.40	43.8	9.30	2.87	1.47	1.14	0.320	0.100	0.026
12	0.740	0.980	0.740	2.40	15.3	24.1	2.63	1.47	1.14	0.420	0.100	0.026
13	0.520	0.980	0.740	2.63	8.88	12.0	2.63	1.63	1.14	0.420	0.100	0.026
14	0.320	0.980	0.520	2.63	6.44	9.30	2.40	1.47	1.47	0.240	0.100	0.026
15	0.320	2.00	0.420	2.63	5.00	9.30	2.40	1.30	1.30	0.420	0.100	0.026
16	0.320	1.80	2.00	2.40	4.42	5.36	2.20	1.14	1.14	0.320	0.060	0.026
17	0.420	1.47	4.42	2.40	4.13	4.42	1.80	1.30	1.14	0.320	0.060	0.026
18	0.620	2.87	3.55	2.40	5.00	3.55	1.80	1.30	0.980	0.240	0.060	0.026
19	0.420	3.55	5.00	3.84	10.6	3.10	1.80	1.14	0.980	0.320	0.060	0.026
20	0.520	3.84	4.42	8.45	18.3	3.10	1.63	1.14	0.980	0.320	0.060	0.026
21	0.520	4.13	3.84	5.36	17.1	3.10	1.80	1.30	0.860	0.320	0.060	0.026
22	0.420	3.33	3.33	4.42	17.1	2.87	1.63	1.14	0.740	0.240	0.060	0.160
23	0.320	2.63	3.10	4.13	16.5	3.33	1.63	0.980	0.860	0.320	0.060	0.100
24	0.240	6.44	3.10	3.84	17.1	3.55	1.47	0.980	0.740	0.240	0.060	0.160
25	0.240	14.8	2.87	3.84	18.3	3.10	1.47	0.980	0.620	0.320	0.026	0.100
26	0.240	14.2	2.87	3.33	24.1	2.87	1.47	0.860	0.620	0.320	0.026	0.240
27	0.320	4.13	3.10	3.10	21.2	2.87	1.47	0.860	0.520	0.320	0.026	0.026
28	0.240	2.00	8.45	3.10	17.1	2.87	1.63	0.740	1.14	0.240	0.026	0.010
29	0.240	1.30	13.6	3.10	-----	2.87	1.63	0.860	1.30	0.240	0.026	0.100
30	0.740	1.14	8.88	3.10	-----	2.87	1.63	0.860	0.980	0.240	0.026	0.980
31	1.47	-----	10.6	2.87	-----	2.87	-----	0.860	-----	0.240	0.026	-----
Maks.	14.2	28.0	18.3	13.6	74.0	68.0	4.71	1.80	2.00	1.47	0.240	0.980
Min.	0.240	0.860	0.160	2.40	2.87	2.87	1.47	0.740	0.420	0.240	0.026	0.010
Ortalama	0.511	3.10	2.89	3.59	11.3	7.25	2.27	1.26	0.912	0.375	0.091	0.080
LT/SN/Km2	2.19	13.3	12.4	15.3	48.2	31.0	9.72	5.37	3.90	1.60	0.389	0.343
AKIM mm.	5.85	34.4	33.1	41.0	117.	83.0	25.2	14.4	10.1	4.30	1.04	0.888
MİL. M3	1.37	8.04	7.75	9.61	27.3	19.4	5.90	3.37	2.36	1.01	0.244	0.208

SU YILI (2006) YILLIK TOPLAM AKIM 86.56 MİLYON M3 370 MM. 11.7 LT/SN/Km2

02. Marmara Havzasi

D02A032 ISIKLAR D. EMİRALİ

YERİ : **MALKARA ŞARKÖY YOLUNUN 23.5 KM.SİNDE EMİRALİ KÖPRÜSÜNDEDİR.G18A3**
27°3'35" Doğu - 40°46'17" Kuzey

YAĞIŞ ALANI : **228,00 km2** **YAKLAŞIK KOT : 67 m**

GÖZLEM SÜRESİ : **01.05.1966 - 30.09.2006**

ORTALAMA AKIMLAR : **Gözlem süresinde 1.423 m3/sn. (36 Yıllık) 2006 Su yılında 1.749 m3/sn.**

ANLIK EN ÇOK VE EN AZ AKIMLAR:

2006 Su yılında anlık ençok akım	**:**	**73.0**	**m3/sn**	**12.03.2006**
2006 Su yılında anlık enaz akım	**:**	**0.016**	**m3/sn**	**27.07.2006**
Gözlem süresinde anlık ençok akım	**:**	**270.**	**m3/sn**	**12.01.1968**
Gözlem süresinde anlık enaz akım	**:**	**0.000**	**m3/sn**	**10.09.1962**

12. Anahtar Eğrisi (Seviyeler cm olarak)

Seviye	Akım	Seviye	Akım	Seviye	Akım	Seviye	Akım
24	0.010	69	1.5	121	9.3	430	157.
32	0.046	80	2.6	129	11.0	510	222.
40	0.150	92	4.2	190	31.0	650	285.
48	0.330	100	5.4	270	65.0		
60	0.840	113	7.5	350	107.		

Akımlar 01 Ekim 2005 'den 30 Eylül 2006' a kadar m3/sn olarak

Gün	Ekim	Kasım	Aralık	Ocak	Şubat	Mart	Nisan	Mayıs	Haziran	Temmuz	Ağustos	Eylül
01	0.084	0.098	0.085	2.10	1.30	5.60	2.00	0.720	0.230	0.100	0.054	0.074
02	0.870	0.084	0.074	1.30	1.70	4.60	1.90	0.670	0.200	0.150	0.046	0.074
03	0.250	0.058	0.100	0.940	2.00	9.00	1.80	0.620	0.190	0.330	0.062	0.085
04	0.115	0.058	0.062	0.940	2.10	4.60	1.70	0.620	0.170	0.170	0.062	0.074
05	0.084	0.058	0.046	0.720	2.10	3.60	1.60	0.620	0.170	0.115	0.062	0.062
06	0.070	0.070	0.046	0.940	1.70	3.00	1.55	0.620	0.190	0.062	0.054	0.062
07	0.070	0.070	0.040	0.670	1.80	9.60	1.50	0.620	0.200	0.046	0.074	0.074
08	0.070	0.070	0.133	0.470	2.10	14.9	1.70	0.620	0.200	0.074	0.074	0.074
09	0.070	0.070	0.150	0.430	2.00	9.00	1.70	0.620	0.330	0.115	0.062	0.085
10	0.058	0.070	0.074	0.430	5.20	7.50	1.50	0.590	0.400	0.085	0.054	0.085
11	0.038	0.070	0.062	0.400	8.20	11.8	1.40	0.590	0.300	0.085	0.046	0.085
12	0.070	0.098	0.046	0.430	6.10	38.9	1.30	0.620	0.250	0.085	0.046	0.085
13	0.084	0.098	0.046	0.430	4.60	14.3	1.25	0.620	0.270	0.085	0.046	0.085
14	0.058	0.084	0.046	0.400	2.90	19.8	1.25	0.590	0.330	0.085	0.040	0.085
15	0.048	0.084	0.046	0.400	2.10	16.7	1.25	0.550	0.370	0.085	0.046	0.085
16	0.048	0.084	0.085	0.400	2.50	21.6	1.20	0.510	0.430	0.100	0.046	0.085
17	0.038	0.098	0.250	0.400	12.0	10.5	1.10	0.470	0.590	0.115	0.046	0.085
18	0.038	0.115	9.30	0.430	38.0	7.00	1.00	0.510	0.370	0.085	0.034	0.085
19	0.038	0.130	4.60	3.70	18.1	5.60	1.00	0.510	0.270	0.115	0.034	0.085
20	0.038	0.420	1.25	2.80	11.0	4.80	0.940	0.470	0.270	0.100	0.034	0.100
21	0.084	0.200	0.780	1.30	7.60	4.30	0.940	0.470	0.230	0.085	0.040	0.250
22	0.084	0.130	0.620	1.40	6.30	3.90	0.890	0.430	0.200	0.100	0.040	0.250
23	0.084	0.460	0.470	1.50	5.20	3.60	0.840	0.370	0.190	0.074	0.054	0.250
24	0.084	2.30	0.370	1.10	5.60	4.10	0.840	0.330	0.170	0.062	0.062	7.80
25	0.084	13.4	0.330	1.00	7.40	3.60	0.780	0.300	0.170	0.046	0.062	1.25
26	0.098	19.5	1.10	1.50	7.00	3.00	0.780	0.270	0.150	0.034	0.074	0.133
27	0.098	1.30	5.00	1.50	9.60	2.70	0.780	0.300	0.133	0.025	0.085	0.062
28	0.084	0.250	3.50	1.20	5.90	2.30	0.720	0.270	0.115	0.034	0.085	0.115
29	0.084	0.550	2.60	0.780	-----	2.30	0.720	0.250	0.115	0.034	0.085	5.60
30	0.084	0.150	2.20	0.670	-----	2.70	0.720	0.230	0.100	0.030	0.074	1.60
31	0.098	-----	7.60	0.890	-----	2.50	-----	0.230	-----	0.046	0.085	-----
Maks.	1.15	52.0	21.2	9.00	45.6	73.0	2.00	0.720	0.720	0.620	0.085	46.5
Min.	0.030	0.058	0.034	0.370	1.30	2.20	0.720	0.230	0.100	0.016	0.034	0.046
Ortalama	0.103	1.34	1.33	1.02	6.50	8.30	1.22	0.491	0.243	0.089	0.057	0.631
LT/SN/Km2	0.453	5.88	5.82	4.47	28.5	36.4	5.36	2.15	1.07	0.390	0.250	2.77
AKIM mm.	1.21	15.2	15.6	12.0	69.0	97.5	13.9	5.76	2.77	1.04	0.670	7.17
MİL. M3	0.277	3.48	3.55	2.73	15.7	22.2	3.17	1.31	0.631	0.238	0.153	1.64

SU YILI (2006) YILLIK TOPLAM AKIM 55.08 MİLYON M3 242 MM. 7.7 LT/SN/Km2

02. Marmara Havzasi

D02A033 KOVANDERE EMİRALİ

YERİ : **MALKARA ŞARKÖY YOLUNUN 22.6 KM. SİNDE EMİRALİ KÖYÜNDEDİR. G 18**
27°3'0" Doğu - 40°46'0" Kuzey

YAĞIŞ ALANI : **175,00 km2** **YAKLAŞIK KOT : 73 m**

GÖZLEM SÜRESİ : **01.05.1966 - 30.09.2006**

ORTALAMA AKIMLAR : **Gözlem süresinde 0.649 m3/sn. (28 Yıllık) 2006 Su yılında 1.088 m3/sn.**

ANLIK EN ÇOK VE EN AZ AKIMLAR:

2006 Su yılında anlık ençok akım	**:**	**29.2**	**m3/sn**	**17.02.2006**
2006 Su yılında anlık enaz akım	**:**	**0.000**	**m3/sn**	**01.10.2005**
Gözlem süresinde anlık ençok akım	**:**	**83.0**	**m3/sn**	**06.03.1971**
Gözlem süresinde anlık enaz akım	**:**	**0.000**	**m3/sn**	**01.10.1968**

İstasyon için kullanılmış anahtar bulunamadı.

Akımlar 01 Ekim 2005 'den 30 Eylül 2006' a kadar m3/sn olarak

Gün	Ekim	Kasım	Aralık	Ocak	Şubat	Mart	Nisan	Mayıs	Haziran	Temmuz	Ağustos	Eylül
01	KURU	0.037	0.680	3.44	1.56	4.28	1.07	0.500	0.180	0.070	KURU	KURU
02	0.050	0.044	0.468	2.20	2.16	2.12	0.990	0.468	0.180	0.090	KURU	KURU
03	0.050	0.060	0.312	1.95	2.51	5.71	0.952	0.468	0.180	0.140	KURU	KURU
04	0.037	0.060	0.256	4.07	2.60	2.33	0.914	0.436	0.160	0.090	KURU	KURU
05	0.031	0.050	0.228	2.20	2.37	1.86	0.876	0.436	0.160	0.060	KURU	KURU
06	0.037	0.050	0.228	4.22	2.08	1.56	0.838	0.436	0.160	0.024	KURU	KURU
07	0.031	0.060	0.200	2.24	2.08	8.92	0.838	0.436	0.160	0.018	KURU	KURU
08	0.024	0.060	0.312	1.56	2.16	11.3	0.952	0.436	0.160	0.018	KURU	KURU
09	0.018	0.060	0.436	1.32	1.95	5.31	0.914	0.536	0.200	0.018	KURU	KURU
10	0.024	0.060	0.256	1.28	2.82	3.91	0.838	0.436	0.228	0.018	KURU	KURU
11	0.060	0.060	0.228	1.21	5.15	4.17	0.800	0.404	0.180	0.018	KURU	KURU
12	0.050	0.060	0.200	1.14	3.96	11.6	0.776	0.608	0.160	0.018	KURU	KURU
13	0.044	0.070	0.200	1.10	2.78	5.20	0.752	0.572	0.160	0.018	KURU	KURU
14	0.044	0.070	0.200	1.10	2.16	8.69	0.728	0.436	0.200	0.024	KURU	KURU
15	0.037	0.060	0.200	1.10	1.74	7.12	0.728	0.372	0.180	0.031	KURU	KURU
16	0.037	0.060	0.284	1.10	1.61	7.44	0.704	0.340	0.228	0.024	KURU	KURU
17	0.037	0.070	0.436	1.03	9.79	3.91	0.680	0.312	0.200	0.018	KURU	KURU
18	0.037	0.100	15.4	0.990	15.8	2.82	0.608	0.340	0.180	0.018	KURU	KURU
19	0.037	0.200	6.02	2.37	5.31	2.33	0.608	0.372	0.160	0.015	KURU	KURU
20	0.037	0.340	2.42	2.16	3.39	2.03	0.572	0.312	0.140	0.015	KURU	KURU
21	0.037	0.100	1.56	1.38	2.46	1.82	0.572	0.312	0.140	0.011	KURU	KURU
22	0.044	0.070	1.42	1.38	1.95	1.65	0.572	0.284	0.120	0.008	KURU	KURU
23	0.037	0.070	1.21	1.28	1.69	1.52	0.536	0.256	0.120	0.001	KURU	0.018
24	0.037	1.14	1.03	0.952	2.20	2.12	0.536	0.256	0.120	0.001	KURU	0.500
25	0.044	8.22	0.990	0.776	4.12	1.61	0.500	0.228	0.090	KURU	KURU	0.436
26	0.044	5.53	1.49	1.10	3.70	1.38	0.500	0.228	0.090	KURU	KURU	0.050
27	0.050	1.61	3.75	1.14	5.31	1.32	0.500	0.228	0.080	KURU	KURU	0.031
28	0.044	1.18	2.64	1.07	3.06	1.25	0.468	0.228	0.080	KURU	KURU	0.090
29	0.037	1.74	3.75	1.03	-----	1.18	0.468	0.228	0.070	KURU	KURU	2.37
30	0.037	0.838	2.69	1.07	-----	1.18	0.500	0.200	0.070	KURU	KURU	0.256
31	0.037	-----	15.1	1.25	-----	1.10	-----	0.200	-----	KURU	KURU	-----
Maks.	0.200	21.6	25.9	8.14	29.2	28.9	1.10	1.03	0.256	0.312	KURU	6.15
Min.	KURU	0.037	0.200	0.704	1.38	1.07	0.468	0.200	0.070	KURU	KURU	KURU
Ortalama	0.038	0.738	2.08	1.62	3.52	3.83	0.710	0.365	0.151	0.025	KURU	0.125
LT/SN/Km2	0.216	4.22	11.9	9.25	20.1	21.9	4.06	2.08	0.864	0.141	0.000	0.714
AKIM mm.	0.578	10.9	31.9	24.8	48.6	58.6	10.5	5.58	2.24	0.378	0.000	1.85
MİL. M3	0.101	1.91	5.58	4.34	8.51	10.3	1.84	0.977	0.392	0.066	0.000	0.324

SU YILI (2006) YILLIK TOPLAM AKIM 34.34 MİLYON M3 196 MM. 6.2 LT/SN/Km2

02. Marmara Havzasi

D02A041 Yalak D. AYAZMA

YERİ : YALOVA KARAMÜRSEL KARAYOLUNUN 13. KM.SİNDE ALTINOVA BELDESİNDEN SAĞA AYRILAN KARADERE KÖYÜ YOLUNUN 3. KM.SİNDEKİ KÖPRÜNÜN 10M. MENBAINDA VE SAĞ SAHİLDEDİR. 29°29'30" Doğu - 40°39'35" Kuzey

YAĞIŞ ALANI : 269,80 km2 **YAKLAŞIK KOT** : 17 m

GÖZLEM SÜRESİ : 14.09.1968 - 30.09.2006

ORTALAMA AKIMLAR : Gözlem süresinde 2.362 m3/sn. (30 Yıllık) 2006 Su yılında 2.820 m3/sn.

ANLIK EN ÇOK VE EN AZ AKIMLAR:

2006 Su yılında anlık ençok akım	:	68.5	m3/sn	11.02.2006
2006 Su yılında anlık enaz akım	:	0.000	m3/sn	15.08.2006
Gözlem süresinde anlık ençok akım	:	320.	m3/sn	10.09.1981
Gözlem süresinde anlık enaz akım	:	0.000	m3/sn	25.08.1977

15. Anahtar Eğrisi (Seviyeler cm olarak)

Seviye	Akım	Seviye	Akım	Seviye	Akım	Seviye	Akım
1	0.001	18	0.490	58	4.9	230	42.0
6	0.044	21	0.690	76	8.0	260	50.0
9	0.110	25	0.990	86	10.0	280	54.0
12	0.210	35	1.9	110	15.0	330	65.0
15	0.340	46	3.2	150	24.0	370	74.0

Akımlar 01 Ekim 2005 'den 30 Eylül 2006' a kadar m3/sn olarak

Gün	Ekim	Kasım	Aralık	Ocak	Şubat	Mart	Nisan	Mayıs	Haziran	Temmuz	Ağustos	Eylül
01	0.185	0.813	1.90	4.15	5.23	10.4	3.50	1.17	0.220	0.070	0.025	KURU
02	0.110	0.410	1.50	3.25	6.05	9.13	3.25	1.17	0.220	0.070	0.025	KURU
03	0.510	0.360	1.40	2.63	6.05	14.5	3.13	1.09	0.255	0.070	0.010	KURU
04	0.220	0.410	1.25	2.25	6.68	11.2	3.00	1.02	0.220	0.070	0.010	KURU
05	0.070	0.877	1.09	2.00	7.03	8.60	2.75	1.02	0.290	0.070	0.010	KURU
06	0.040	0.940	0.940	1.80	8.60	7.38	2.75	1.02	0.255	0.055	0.010	KURU
07	0.040	1.60	0.813	1.80	7.73	7.38	2.63	1.02	0.220	0.055	0.010	KURU
08	0.040	0.877	0.813	4.15	7.55	13.6	2.50	1.02	0.185	0.055	0.010	KURU
09	0.040	0.510	1.09	10.2	7.20	14.5	2.75	0.940	0.220	0.055	0.010	KURU
10	0.025	0.360	0.813	4.90	19.6	12.2	2.50	0.940	0.220	0.055	0.010	KURU
11	0.040	0.290	0.877	3.50	44.4	17.4	2.38	0.940	0.255	0.055	0.010	KURU
12	0.055	0.255	0.940	3.38	20.8	23.3	2.25	0.813	0.255	0.055	0.010	KURU
13	0.110	0.255	0.940	4.45	14.7	13.8	2.13	0.750	0.325	0.055	0.010	KURU
14	0.110	0.290	0.877	4.00	12.2	14.0	2.00	0.750	0.290	0.040	0.010	KURU
15	0.070	0.560	0.813	3.38	10.2	15.4	2.00	0.687	0.255	0.040	KURU	KURU
16	0.110	0.623	1.02	2.88	8.78	11.2	1.90	0.687	0.220	0.040	KURU	KURU
17	0.185	0.410	2.88	2.50	8.43	10.0	1.90	0.687	0.185	0.040	KURU	KURU
18	0.220	0.460	2.63	2.25	16.0	8.78	1.80	0.623	0.185	0.040	KURU	KURU
19	0.220	1.17	8.25	4.30	19.0	8.25	1.80	0.560	0.185	0.040	KURU	KURU
20	0.220	4.60	5.40	7.90	19.0	7.38	1.70	0.560	0.185	0.040	KURU	KURU
21	0.220	7.20	3.88	5.40	14.5	6.68	1.60	0.560	0.185	0.040	KURU	KURU
22	0.220	3.00	3.13	5.40	11.6	6.05	1.60	0.510	0.185	0.040	KURU	KURU
23	0.185	2.50	2.88	5.40	11.0	5.73	1.50	0.460	0.150	0.040	KURU	KURU
24	0.110	8.25	3.00	4.75	10.4	5.57	1.50	0.460	0.150	0.040	KURU	KURU
25	0.110	6.50	2.88	4.45	10.6	5.23	1.40	0.410	0.150	0.040	KURU	KURU
26	0.110	8.78	4.00	4.30	14.2	4.75	1.40	0.360	0.150	0.025	KURU	KURU
27	0.150	4.15	7.38	4.00	17.2	4.45	1.32	0.325	0.110	0.025	KURU	KURU
28	0.185	2.88	11.6	3.88	11.8	4.15	1.17	0.325	0.110	0.025	KURU	KURU
29	0.185	3.25	8.25	4.00	-----	4.00	1.09	0.290	0.070	0.025	KURU	KURU
30	0.290	2.63	5.23	4.00	-----	3.75	1.09	0.290	0.070	0.025	KURU	KURU
31	0.560	-----	4.75	4.30	-----	3.63	-----	0.255	-----	0.025	KURU	-----
Maks.	0.750	19.6	13.6	12.8	68.5	40.1	3.50	2.00	0.510	0.070	0.025	KURU
Min.	0.025	0.220	0.687	1.60	4.90	3.63	1.09	0.255	0.070	0.025	KURU	KURU
Ortalama	0.160	2.17	3.01	4.05	12.7	9.43	2.08	0.700	0.199	0.046	0.005	KURU
LT/SN/Km2	0.591	8.06	11.1	15.0	47.2	35.0	7.70	2.60	0.738	0.170	0.020	0.000
AKIM mm.	1.58	20.9	29.9	40.2	114.	93.6	19.9	6.95	1.91	0.455	0.054	0.000
MİL. M3	0.427	5.63	8.05	10.8	30.8	25.3	5.38	1.88	0.516	0.123	0.015	0.000

SU YILI (2006) YILLIK TOPLAM AKIM 88.92 MİLYON M3 330 MM. 10.5 LT/SN/Km2

02. Marmara Havzasi

D02A047 MOLOVA D. PİRİNÇCİKÖY

YERİ : İSTANBUL- KEMERBURGAZDAN PİRİNÇCİKÖY İSTİKAMETİNE 7 KM GİDİLİR. İSTASYON KÖY GİRİŞİNDEDİR
PAFTA 25.000: İST-F21-C1
28°51'10" Doğu - 41°9'47" Kuzey

YAĞIŞ ALANI : 111,80 km2 **YAKLAŞIK KOT** : 25 m

GÖZLEM SÜRESİ : 15.03.1969 - 30.09.2006

ORTALAMA AKIMLAR : Gözlem süresinde 2.817 m3/sn. (37 Yıllık) 2006 Su yılında 1.981 m3/sn.

ANLIK EN ÇOK VE EN AZ AKIMLAR:

2006 Su yılında anlık ençok akım	:	103.	m3/sn	18.12.2005
2006 Su yılında anlık enaz akım	:	0.000	m3/sn	16.07.2006
Gözlem süresinde anlık ençok akım	:	165.	m3/sn	12.12.1976
Gözlem süresinde anlık enaz akım	:	0.000	m3/sn	07.07.1969

10. Anahtar Eğrisi (Seviyeler cm olarak)

Seviye	Akım	Seviye	Akım	Seviye	Akım	Seviye	Akım
13	0.000	50	1.4	250	48.6	420	186.
17	0.005	90	5.4	290	68.0	430	197.
21	0.023	130	11.4	330	96.0	440	208.
25	0.072	170	20.0	370	134.	450	220.
29	0.166	210	32.2	410	175.		

Akımlar 01 Ekim 2005 'den 30 Eylül 2006' a kadar m3/sn olarak

Gün	Ekim	Kasım	Aralık	Ocak	Şubat	Mart	Nisan	Mayıs	Haziran	Temmuz	Ağustos	Eylül
01	0.028	0.386	0.524	2.61	3.68	4.56	1.47	0.273	0.055	0.008	KURU	0.023
02	0.070	0.272	0.524	2.43	3.89	3.89	1.24	0.273	0.055	0.008	KURU	0.032
03	0.140	0.570	6.52	2.25	3.68	6.05	1.17	0.234	0.092	0.003	KURU	0.042
04	0.170	0.524	1.93	2.16	3.26	3.89	1.10	0.234	0.072	0.001	KURU	0.032
05	0.037	0.306	1.25	2.08	3.26	2.88	1.03	0.273	0.055	0.002	KURU	0.016
06	0.028	0.238	0.900	1.99	15.6	2.61	0.954	0.273	0.042	0.001	KURU	0.008
07	0.028	0.170	0.768	3.57	6.57	6.31	0.812	0.273	0.042	0.003	KURU	0.003
08	0.047	0.170	0.768	3.99	4.92	29.4	0.883	0.273	0.072	0.003	KURU	0.002
09	0.037	0.140	0.900	3.57	4.20	14.4	1.03	0.312	0.092	0.002	KURU	0.001
10	0.021	0.116	0.636	4.32	19.0	7.96	0.883	0.273	0.115	0.001	KURU	0.001
11	0.015	0.094	0.524	6.70	35.2	5.79	0.741	0.273	0.072	0.005	KURU	0.016
12	0.028	0.094	0.478	5.40	20.8	5.04	0.614	0.234	0.072	0.001	KURU	0.072
13	0.015	0.272	0.386	3.99	13.1	3.47	0.502	0.234	0.092	0.002	KURU	0.023
14	0.015	0.570	0.340	3.15	7.40	3.57	0.614	0.234	0.234	0.002	KURU	0.016
15	0.011	0.432	0.340	2.61	6.57	7.82	0.558	0.234	0.390	0.002	KURU	0.011
16	0.037	0.272	0.900	2.43	5.16	5.28	0.502	0.234	0.166	0.001	KURU	0.008
17	0.060	0.204	1.34	2.34	7.26	3.57	0.502	0.273	0.115	KURU	KURU	0.011
18	0.047	1.18	53.7	2.25	15.0	2.52	0.446	0.273	0.055	KURU	KURU	0.008
19	0.037	1.11	50.9	3.47	9.38	1.99	0.390	0.312	0.042	KURU	KURU	0.011
20	0.070	3.98	8.26	4.20	6.70	1.82	0.351	0.273	0.016	KURU	KURU	0.023
21	0.028	2.60	3.99	3.36	4.68	1.64	0.351	0.234	0.011	KURU	KURU	0.016
22	0.028	0.970	2.70	2.97	4.10	1.55	0.351	0.195	0.042	KURU	KURU	0.023
23	0.021	0.970	2.08	2.70	3.99	1.38	0.312	0.234	0.023	KURU	KURU	7.26
24	0.021	2.70	2.52	2.52	4.10	1.64	0.312	0.195	0.016	KURU	KURU	8.74
25	0.015	6.52	2.61	2.43	7.96	1.82	0.351	0.166	0.011	KURU	KURU	1.90
26	0.015	4.68	2.52	2.34	6.44	1.64	0.558	0.140	0.008	KURU	KURU	0.741
27	0.028	1.76	2.43	2.25	11.2	1.38	0.390	0.166	0.005	KURU	KURU	0.446
28	0.028	1.04	2.34	2.25	6.44	1.24	0.312	0.140	0.008	KURU	KURU	0.351
29	0.028	0.834	2.25	2.34	-----	1.17	0.273	0.115	0.016	KURU	KURU	0.558
30	0.524	0.636	2.16	2.25	-----	1.38	0.312	0.092	0.008	KURU	KURU	0.558
31	1.51	-----	3.15	2.25	-----	1.82	-----	0.072	-----	KURU	0.001	-----
Maks.	3.87	21.3	103.	11.4	51.8	36.8	2.70	0.558	0.670	0.016	0.005	75.4
Min.	0.011	0.070	0.340	1.99	2.79	1.17	0.273	0.055	0.003	KURU	KURU	0.001
Ortalama	0.103	1.13	5.18	3.01	8.70	4.50	0.644	0.226	0.070	0.001	0.000	0.698
LT/SN/Km2	0.920	10.1	46.3	26.9	77.8	40.2	5.76	2.02	0.624	0.013	0.000	6.25
AKIM mm.	2.46	26.1	124.	72.0	188.	108.	14.9	5.42	1.62	0.035	0.001	16.2
MİL. M3	0.275	2.92	13.9	8.05	21.0	12.1	1.67	0.606	0.181	0.004	0.000	1.81

SU YILI (2006) YILLIK TOPLAM AKIM 62.52 MİLYON M3 559 MM. 17.7 LT/SN/Km2

02. Marmara Havzasi

D02A055 OZAN D. BIÇKIDERE

YERİ : İSTANBUL-ŞİLE YOLUNUN KÖMÜRLÜK KÖY- BIÇKIDERE SAPAĞINDAN SAPILIR. BIÇKIDERE KÖYÜNDEN 2.5 KM DEVAM EDİLEREK İSTASYONA VARILIR. PAFTA 25.000: İST-F22-C3 29°28'9" Doğu - 41°3'4" Kuzey

YAĞIŞ ALANI : 87,00 km2 **YAKLAŞIK KOT** : 70 m

GÖZLEM SÜRESİ : 01.10.1974 - 30.09.2006

ORTALAMA AKIMLAR : Gözlem süresinde 2.671 m3/sn. (25 Yıllık) 2006 Su yılında 1.906 m3/sn.

ANLIK EN ÇOK VE EN AZ AKIMLAR:

2006 Su yılında anlık ençok akım	:	52.0	m3/sn	11.02.2006
2006 Su yılında anlık enaz akım	:	0.002	m3/sn	20.08.2006
Gözlem süresinde anlık ençok akım	:	148.	m3/sn	13.08.1997
Gözlem süresinde anlık enaz akım	:	0.000	m3/sn	24.07.1975

12. Anahtar Eğrisi (Seviyeler cm olarak)

Seviye	Akım	Seviye	Akım	Seviye	Akım	Seviye	Akım
2	0.000	17	0.285	120	27.2	270	167.
5	0.007	20	0.410	150	45.0	280	178.
8	0.036	35	1.4	180	68.0	290	189.
11	0.089	60	4.5	210	101.	300	200.
14	0.170	90	12.5	240	134.		

Akımlar 01 Ekim 2005 'den 30 Eylül 2006' a kadar m3/sn olarak

Gün	Ekim	Kasım	Aralık	Ocak	Şubat	Mart	Nisan	Mayıs	Haziran	Temmuz	Ağustos	Eylül
01	0.089	2.01	1.09	3.45	3.45	3.30	0.626	0.236	0.068	0.023	0.014	0.007
02	0.068	0.626	0.872	2.34	4.69	2.67	0.626	0.285	0.089	0.023	0.014	0.036
03	0.068	0.365	2.56	1.81	5.26	6.65	0.572	0.236	0.068	0.014	0.023	0.023
04	0.051	0.315	2.45	1.43	5.64	4.50	0.572	0.236	0.068	0.014	0.023	0.014
05	0.068	0.626	1.81	1.17	5.07	2.89	0.518	0.236	0.068	0.014	0.014	0.014
06	0.068	2.34	1.34	1.09	9.98	2.23	0.518	0.236	0.068	0.014	0.014	0.007
07	0.068	1.43	1.00	1.00	6.02	3.15	0.518	0.236	0.068	0.014	0.014	0.007
08	0.068	0.808	0.872	1.81	4.20	11.4	0.464	0.236	0.051	0.014	0.023	0.007
09	0.068	0.572	1.71	8.15	3.45	9.26	0.518	0.236	0.068	0.014	0.036	0.007
10	0.068	0.410	1.26	10.7	8.15	6.02	0.464	0.205	1.34	0.023	0.023	0.014
11	0.068	0.315	1.71	10.7	28.4	9.98	0.464	0.205	0.315	0.014	0.014	0.023
12	0.068	0.285	2.45	6.21	8.90	9.62	0.464	0.170	0.170	0.014	0.023	0.014
13	0.068	0.236	2.01	7.65	5.83	4.35	0.410	0.170	0.114	0.014	0.014	0.007
14	0.068	0.572	1.43	12.5	4.35	3.45	0.410	0.170	0.626	0.014	0.007	0.007
15	0.051	1.81	1.26	7.15	3.60	4.35	0.365	0.170	0.410	0.014	0.007	0.014
16	0.089	1.26	1.43	4.20	3.00	3.45	0.365	0.140	0.236	0.014	0.007	0.014
17	0.089	0.808	3.75	2.89	3.90	2.67	0.365	0.140	0.140	0.014	0.007	0.014
18	0.068	0.680	5.45	2.12	26.7	2.23	0.365	0.140	0.114	0.014	0.007	0.014
19	0.089	0.808	25.6	3.90	23.9	1.81	0.365	0.140	0.068	0.014	0.007	0.014
20	0.089	8.90	6.90	7.65	23.4	1.52	0.315	0.114	0.051	0.014	0.002	0.014
21	0.089	15.1	3.60	4.69	15.1	1.34	0.315	0.114	0.051	0.014	0.002	0.014
22	0.114	3.15	2.56	4.69	11.4	1.09	0.315	0.114	0.036	0.014	0.002	0.023
23	0.114	2.01	2.23	5.45	8.15	1.00	0.315	0.114	0.036	0.014	0.007	0.036
24	0.089	4.69	2.23	3.75	6.40	1.09	0.315	0.114	0.023	0.014	0.002	0.023
25	0.114	3.75	2.12	3.15	5.26	1.00	0.285	0.114	0.036	0.014	0.007	0.036
26	0.089	8.40	2.89	2.67	6.02	0.936	0.285	0.089	0.023	0.023	0.007	0.023
27	0.089	2.89	6.02	2.23	4.88	0.872	0.236	0.089	0.023	0.014	0.007	0.023
28	0.089	1.71	8.40	2.12	3.90	0.872	0.236	0.089	0.023	0.014	0.007	0.023
29	0.140	1.62	4.50	2.23	-----	0.808	0.236	0.068	0.023	0.014	0.036	0.036
30	0.285	1.43	2.56	2.23	-----	0.808	0.285	0.068	0.023	0.014	0.002	0.036
31	3.60	-----	3.45	2.67	-----	0.808	-----	0.068	-----	0.014	0.002	-----
Maks.	5.26	43.2	37.8	16.4	52.0	22.8	0.680	0.285	7.90	0.068	0.205	0.140
Min.	0.051	0.236	0.808	0.936	3.00	0.744	0.236	0.068	0.014	0.007	0.002	0.007
Ortalama	0.201	2.33	3.47	4.32	8.89	3.42	0.404	0.161	0.150	0.015	0.012	0.018
LT/SN/Km2	2.31	26.8	39.9	49.6	102.	39.3	4.64	1.85	1.72	0.174	0.139	0.208
AKIM mm.	6.20	69.4	107.	133.	247.	105.	12.0	4.94	4.47	0.467	0.371	0.540
MİL. M3	0.539	6.04	9.29	11.6	21.5	9.17	1.05	0.430	0.389	0.041	0.032	0.047

SU YILI (2006) YILLIK TOPLAM AKIM 60.13 MİLYON M3 691 MM. 21.9 LT/SN/Km2

02. Marmara Havzasi

D02A057 PAPUÇ D. KIZILAGAÇ

YERİ : **KIZILAĞAÇ-KOMURKOY YOLUNDA 2. KMDE YOLUN S YOLUNUN 8 KM.SİNDEDİR. E 19**
27°53'0" Doğu - 41°40'55" Kuzey

YAĞIŞ ALANI : **83,50 km2** **YAKLAŞIK KOT : 120 m**

GÖZLEM SÜRESİ : **17.06.1975 - 30.09.2006**

ORTALAMA AKIMLAR : **Gözlem süresinde 1.035 m3/sn. (29 Yıllık) 2006 Su yılında 1.736 m3/sn.**

ANLIK EN ÇOK VE EN AZ AKIMLAR:

2006 Su yılında anlık ençok akım	**:**	**59.0**	**m3/sn**	**03.07.2006**
2006 Su yılında anlık enaz akım	**:**	**0.220**	**m3/sn**	**01.10.2005**
Gözlem süresinde anlık ençok akım	**:**	**190.**	**m3/sn**	**21.08.1984**
Gözlem süresinde anlık enaz akım	**:**	**0.000**	**m3/sn**	**02.10.1994**

İstasyon için kullanılmış anahtar bulunamadı.

Akımlar 01 Ekim 2005 'den 30 Eylül 2006' a kadar m3/sn olarak

Gün	Ekim	Kasım	Aralık	Ocak	Şubat	Mart	Nisan	Mayıs	Haziran	Temmuz	Ağustos	Eylül
01	0.220	0.370	0.530	3.10	2.80	8.60	3.20	0.830	0.530	0.490	0.510	0.470
02	0.410	0.370	0.530	1.80	2.80	6.20	3.10	0.830	0.530	1.30	0.510	0.470
03	0.450	0.370	0.650	1.30	3.00	7.80	3.10	0.790	0.530	15.2	0.510	0.470
04	0.270	0.370	0.530	1.15	3.00	5.70	3.00	0.790	0.530	2.50	0.510	0.470
05	0.240	0.370	0.530	0.970	3.00	5.10	2.80	0.790	0.530	1.50	0.510	0.470
06	0.240	0.370	0.450	2.30	2.60	4.70	2.20	0.790	0.600	1.10	0.510	0.470
07	0.240	0.370	0.410	3.90	3.20	7.30	1.40	0.790	0.530	1.05	0.510	0.470
08	0.240	0.370	0.650	1.70	3.10	6.80	1.50	0.750	0.530	0.800	0.510	0.470
09	0.240	0.370	0.830	1.23	3.10	5.70	1.40	0.830	4.80	0.650	0.510	0.470
10	0.240	0.370	0.530	0.970	3.20	5.70	1.30	0.790	0.970	0.550	0.510	0.470
11	0.240	0.370	0.570	0.920	3.40	11.5	1.30	0.790	0.750	0.550	0.510	0.470
12	0.240	0.370	0.880	0.920	3.20	16.7	1.23	0.790	0.650	0.550	0.510	0.470
13	0.240	0.370	0.600	0.830	2.80	9.70	1.23	0.790	1.15	0.550	0.510	0.470
14	0.300	0.370	0.530	0.750	2.70	8.20	1.15	0.790	1.15	0.550	0.510	0.470
15	0.300	0.370	0.600	0.700	2.60	7.50	1.15	0.750	0.750	0.550	0.510	0.470
16	0.300	0.370	0.700	0.700	2.40	6.80	1.05	0.750	0.750	0.550	0.510	0.470
17	0.300	0.370	0.700	0.700	3.70	6.20	1.05	0.750	0.700	0.550	0.510	0.470
18	0.300	0.750	0.970	0.750	11.8	5.90	1.05	0.700	0.600	0.550	0.510	0.470
19	0.300	0.650	0.830	4.00	10.0	5.50	0.970	0.700	0.570	0.550	0.470	0.470
20	0.300	1.23	0.750	2.80	10.5	5.10	0.970	0.700	0.570	0.550	0.470	0.470
21	0.300	0.750	0.700	1.95	8.80	5.10	0.970	0.650	0.570	0.550	0.470	0.470
22	0.300	0.490	0.600	1.95	7.90	4.70	0.920	0.650	0.570	0.550	0.470	0.470
23	0.300	0.300	0.570	1.70	6.60	4.50	0.920	0.600	0.570	0.550	0.470	0.470
24	0.300	3.70	0.530	1.30	5.90	4.70	0.920	0.600	0.530	0.550	0.470	0.470
25	0.300	6.40	0.530	1.70	7.90	4.20	0.880	0.570	0.530	0.550	0.470	0.470
26	0.300	1.70	0.530	2.80	10.5	3.90	0.880	0.570	0.530	0.550	0.470	0.470
27	0.300	0.700	0.530	3.70	9.55	3.70	0.880	0.570	0.530	0.510	0.470	0.470
28	0.300	0.650	14.0	3.20	7.00	3.60	0.880	0.570	0.530	0.510	0.470	0.470
29	0.300	0.570	5.90	2.80	-----	3.60	0.880	0.570	0.490	0.510	0.470	0.700
30	0.340	0.570	3.40	2.70	-----	3.50	0.880	0.570	0.490	0.510	0.470	0.470
31	0.340	-----	8.80	2.80	-----	3.40	-----	0.530	-----	0.510	0.470	-----
Maks.	1.40	10.8	31.7	8.40	16.7	29.1	3.20	0.920	17.5	59.0	0.510	1.45
Min.	0.220	0.300	0.410	0.700	1.95	3.20	0.830	0.530	0.490	0.490	0.470	0.470
Ortalama	0.290	0.825	1.58	1.87	5.25	6.18	1.44	0.708	0.769	1.18	0.493	0.478
LT/SN/Km2	3.47	9.88	18.9	22.4	62.9	74.0	17.2	8.48	9.21	14.1	5.91	5.72
AKIM mm.	9.30	25.6	50.6	60.1	152.	198.	44.7	22.7	23.9	37.8	15.8	14.8
MİL. M3	0.777	2.14	4.22	5.02	12.7	16.6	3.73	1.90	1.99	3.15	1.32	1.24

SU YILI (2006) YILLIK TOPLAM AKIM 54.79 MİLYON M3 656 MM. 20.8 LT/SN/Km2

02. Marmara Havzasi

D02A065 Sariçay Nisankaya

YERİ : **ÇANAKKALE ÇAN YOLUNUN 20. KM'SİNDEDİR.**
26°34'54" Doğu - 40°3'28" Kuzey

YAĞIŞ ALANI : **215.00 km2** **YAKLAŞIK KOT : 70 m**

GÖZLEM SÜRESİ : **01.10.1977 - 30.09.2006**

ORTALAMA AKIMLAR : **Gözlem süresinde 1.006 m3/sn. (29 Yıllık) 2006 Su yılında 0.921 m3/sn.**

ANLIK EN ÇOK VE EN AZ AKIMLAR:

2006 Su yılında anlık ençok akım	:	**28.3**	**m3/sn**	**25.11.2005**
2006 Su yılında anlık enaz akım	:	**0.000**	**m3/sn**	**01.10.2005**
Gözlem süresinde anlık ençok akım	:	**220.**	**m3/sn**	**07.12.1997**
Gözlem süresinde anlık enaz akım	:	**0.000**	**m3/sn**	**01.10.1984**

6. Anahtar Eğrisi (Seviyeler cm olarak)

Seviye	Akım	Seviye	Akım	Seviye	Akım	Seviye	Akım
1	0.018	16	2.2	32	6.8	150	120.
4	0.155	19	2.9	44	13.0	180	156.
7	0.460	22	3.6	58	23.0	220	212.
10	0.960	25	4.4	80	43.0	230	226.
13	1.6	28	5.3	110	74.0	240	241.

Akımlar 01 Ekim 2005 'den 30 Eylül 2006' a kadar m3/sn olarak

Gün	Ekim	Kasım	Aralık	Ocak	Şubat	Mart	Nisan	Mayıs	Haziran	Temmuz	Ağustos	Eylül
01	KURU	KURU	1.00	2.45	3.35	2.65	0.640	0.360	0.068	KURU	KURU	KURU
02	KURU	KURU	1.00	1.21	3.85	2.00	0.640	0.360	0.068	KURU	KURU	KURU
03	KURU	KURU	1.00	0.800	3.85	3.15	0.640	0.360	0.068	KURU	KURU	KURU
04	KURU	KURU	0.800	0.640	3.35	2.45	0.500	0.360	0.068	KURU	KURU	KURU
05	KURU	KURU	0.800	0.800	3.60	2.00	0.500	0.360	0.068	KURU	KURU	KURU
06	KURU	KURU	0.800	1.21	10.5	1.75	0.500	0.360	0.068	KURU	KURU	KURU
07	KURU	KURU	0.640	0.800	4.70	2.90	0.500	0.270	0.068	KURU	KURU	KURU
08	KURU	KURU	0.640	0.800	3.15	11.8	0.500	0.360	0.068	KURU	KURU	KURU
09	KURU	KURU	0.640	0.640	2.45	4.40	0.360	0.360	0.115	KURU	KURU	KURU
10	KURU	KURU	0.800	0.640	7.23	3.15	0.360	0.360	0.115	KURU	KURU	KURU
11	KURU	KURU	0.800	0.640	11.8	7.67	0.360	0.270	0.115	KURU	KURU	KURU
12	KURU	KURU	0.800	0.640	5.70	5.70	0.360	0.270	0.115	KURU	KURU	KURU
13	KURU	KURU	0.640	0.800	3.35	4.10	0.360	0.360	0.068	KURU	KURU	KURU
14	KURU	KURU	0.640	0.800	2.65	2.90	0.360	0.360	0.068	KURU	KURU	KURU
15	KURU	KURU	0.800	0.640	2.00	2.65	0.360	0.270	0.068	KURU	KURU	KURU
16	KURU	KURU	0.800	0.800	1.75	2.45	0.360	0.270	0.068	KURU	KURU	KURU
17	KURU	KURU	1.00	0.800	1.75	2.45	0.360	0.180	0.068	KURU	KURU	KURU
18	KURU	KURU	1.21	0.800	7.23	2.20	0.500	0.270	0.035	KURU	KURU	KURU
19	KURU	KURU	1.21	3.85	5.30	2.20	0.500	0.360	0.035	KURU	KURU	KURU
20	KURU	KURU	1.42	5.00	3.85	2.00	0.500	0.270	0.035	KURU	KURU	KURU
21	KURU	0.115	1.00	2.45	2.90	2.00	0.500	0.270	0.035	KURU	KURU	KURU
22	KURU	0.115	0.800	2.00	2.00	2.00	0.500	0.180	0.035	KURU	KURU	KURU
23	KURU	0.270	0.640	2.65	1.75	2.00	0.360	0.180	0.035	KURU	KURU	KURU
24	KURU	4.10	0.500	2.20	1.42	1.75	0.360	0.180	0.013	KURU	KURU	KURU
25	KURU	8.10	0.360	2.20	7.23	2.20	0.360	0.180	KURU	KURU	KURU	KURU
26	KURU	3.85	0.270	2.20	8.58	2.00	0.360	0.180	KURU	KURU	KURU	KURU
27	KURU	2.20	0.360	1.75	4.70	1.42	0.360	0.180	KURU	KURU	KURU	KURU
28	KURU	1.21	0.640	2.00	3.35	1.00	0.360	0.180	KURU	KURU	KURU	KURU
29	KURU	1.00	2.20	2.00	-----	0.800	0.360	0.180	KURU	KURU	KURU	KURU
30	KURU	1.00	1.21	2.45	-----	0.800	0.360	0.180	KURU	KURU	KURU	KURU
31	KURU	-----	5.30	2.90	-----	0.800	-----	0.180	-----	KURU	KURU	-----
Maks.	KURU	28.3	15.5	18.5	19.3	28.3	0.800	0.360	0.115	KURU	KURU	KURU
Min.	KURU	KURU	0.180	0.500	1.21	0.800	0.270	0.068	KURU	KURU	KURU	KURU
Ortalama	KURU	0.732	0.991	1.60	4.41	2.82	0.435	0.273	0.052	KURU	KURU	KURU
LT/SN/Km2	0.000	3.40	4.61	7.44	20.5	13.1	2.02	1.27	0.243	0.000	0.000	0.000
AKIM mm.	0.000	8.82	12.3	19.9	49.6	35.1	5.24	3.40	0.630	0.000	0.000	0.000
MİL. M3	0.000	1.90	2.65	4.28	10.7	7.55	1.13	0.731	0.135	0.000	0.000	0.000

SU YILI (2006) YILLIK TOPLAM AKIM 29.08 MİLYON M3 135 MM. 4.3 LT/SN/Km2

02. Marmara Havzasi

D02A067 GÖÇBEYLİ D. GÖÇBEYLİ

YERİ : İSTANBUL - KOÇAELİ TEM OTOYOLUNDAN, AKFIRAT-ORHANLI İSTİKAMETİNE SAPILARAK, GÖÇBEYLİ KÖYÜ İSTIKAMETINDE, KÖY GİRİŞİNDEKİ KÖPRÜDEDİR. PAFTA 25.000:BUR-G22-B2
29°27'17" Doğu - 40°58'4" Kuzey

YAĞIŞ ALANI : 145,70 km2 **YAKLAŞIK KOT :** 102 m

GÖZLEM SÜRESİ : 16.03.1978 - 30.09.2006

ORTALAMA AKIMLAR : Gözlem süresinde 1.579 m3/sn. (23 Yıllık) 2006 Su yılında 2.054 m3/sn.

ANLIK EN ÇOK VE EN AZ AKIMLAR:

2006 Su yılında anlık ençok akım	:	64.9	m3/sn	11.02.2006
2006 Su yılında anlık enaz akım	:	0.000	m3/sn	01.08.2006
Gözlem süresinde anlık ençok akım	:	77.4	m3/sn	15.12.1981
Gözlem süresinde anlık enaz akım	:	0.000	m3/sn	31.07.1985

8. Anahtar Eğrisi (Seviyeler cm olarak)

Seviye	Akım	Seviye	Akım	Seviye	Akım	Seviye	Akım
12	0.000	90	7.6	240	35.9	390	79.0
15	0.005	120	11.1	270	44.0	420	88.0
18	0.040	150	15.0	300	52.2	430	91.0
30	0.920	180	20.4	330	61.0	440	94.0
60	4.2	210	27.9	360	70.0	450	97.0

Akımlar 01 Ekim 2005 'den 30 Eylül 2006' a kadar m3/sn olarak

Gün	Ekim	Kasım	Aralık	Ocak	Şubat	Mart	Nisan	Mayıs	Haziran	Temmuz	Ağustos	Eylül
01	0.248	1.35	1.88	5.61	4.59	4.93	0.836	0.416	0.020	0.020	0.001	0.164
02	0.164	0.668	1.78	3.57	6.85	3.35	0.752	0.332	0.060	0.020	KURU	0.248
03	0.248	0.668	3.91	3.01	7.19	13.0	0.752	0.416	0.040	0.020	KURU	0.164
04	0.248	0.668	2.44	2.89	7.08	6.28	0.752	0.332	0.020	0.020	KURU	0.164
05	0.164	0.752	2.22	2.67	5.95	3.57	0.668	0.332	0.020	0.002	KURU	0.080
06	0.164	1.24	1.88	2.67	11.3	2.67	0.668	0.332	0.060	0.005	KURU	0.080
07	0.248	1.03	1.67	2.44	6.96	6.06	0.584	0.248	0.080	0.001	KURU	0.060
08	0.248	0.752	1.78	2.67	5.61	11.7	0.668	0.332	0.060	0.005	KURU	0.060
09	0.248	0.668	2.56	5.27	5.15	12.2	0.668	0.248	0.060	0.010	KURU	0.060
10	0.248	0.584	1.78	7.64	17.1	7.64	0.668	0.248	0.248	0.080	KURU	0.080
11	0.248	0.500	1.78	6.17	35.6	7.30	0.668	0.248	0.164	0.164	KURU	0.164
12	0.248	0.500	1.78	6.85	11.7	7.08	0.584	0.332	0.164	0.164	0.001	0.060
13	0.248	0.416	1.67	8.21	8.10	4.48	0.584	0.584	0.248	0.040	0.005	0.060
14	0.164	0.836	1.56	9.69	5.83	5.15	0.584	0.500	0.584	0.020	0.020	0.060
15	0.248	1.13	1.46	5.95	4.59	6.06	0.500	0.416	0.248	0.060	0.010	0.060
16	0.332	0.752	2.78	4.02	3.80	3.80	0.500	0.332	0.080	0.002	0.002	0.060
17	0.332	0.668	3.35	3.01	5.72	3.01	0.500	0.332	0.060	0.001	0.001	0.060
18	0.248	0.836	3.12	2.89	15.8	2.67	0.416	0.248	0.060	0.005	KURU	0.040
19	0.248	1.13	16.0	13.7	15.6	2.33	0.416	0.248	0.020	0.020	KURU	0.040
20	0.416	6.74	6.62	9.81	13.7	2.22	0.500	0.164	0.040	0.010	KURU	0.040
21	0.248	9.01	3.91	6.40	9.58	1.99	0.500	0.164	0.040	0.001	KURU	0.060
22	0.248	2.44	3.01	5.04	6.85	1.88	0.416	0.248	0.040	0.001	KURU	0.080
23	0.248	2.22	3.12	4.59	4.93	1.78	0.416	0.164	0.040	0.001	KURU	0.080
24	0.248	3.69	3.12	3.69	3.91	1.99	0.416	0.080	0.040	0.002	KURU	0.164
25	0.248	7.19	3.01	3.57	3.69	1.88	0.416	0.060	0.010	0.001	KURU	0.248
26	0.248	11.3	4.14	3.46	8.55	1.78	0.332	0.060	0.020	0.002	KURU	0.248
27	0.248	3.69	5.38	3.23	6.17	1.56	0.332	0.060	0.020	0.001	0.001	0.164
28	0.248	2.56	6.40	3.23	4.25	1.03	0.332	0.060	0.020	0.005	0.002	0.164
29	0.332	2.44	4.14	3.12	-----	0.920	0.332	0.040	0.040	0.010	0.164	0.080
30	0.668	2.10	3.35	3.12	-----	0.920	0.416	0.040	0.040	0.005	0.060	0.080
31	1.99	-----	9.24	3.35	-----	0.920	-----	0.020	-----	0.001	0.080	-----
Maks.	2.67	29.2	24.8	32.4	64.9	36.4	0.836	0.668	0.836	0.332	0.416	0.416
Min.	0.164	0.416	1.35	2.44	3.23	0.836	0.332	0.010	0.010	0.001	KURU	0.010
Ortalama	0.320	2.28	3.58	4.89	8.79	4.26	0.539	0.246	0.088	0.023	0.011	0.106
LT/SN/Km2	2.20	15.7	24.5	33.6	60.3	29.3	3.70	1.69	0.605	0.155	0.077	0.726
AKIM mm.	5.89	40.6	65.7	89.9	146.	78.4	9.59	4.53	1.57	0.415	0.206	1.88
MİL. M3	0.858	5.92	9.58	13.1	21.3	11.4	1.40	0.660	0.229	0.060	0.030	0.274

SU YILI (2006) YILLIK TOPLAM AKIM 64.81 MİLYON M3 445 MM. 14.1 LT/SN/Km2

02. Marmara Havzasi

D02A069 KAYNARCA DERESİ Cihadiye

YERİ : **BİGA-CIHADIYE KÖYÜ' NDEKI KÖPRÜDEDIR.**
27°6'53" Doğu - 40°11'28" Kuzey

YAĞIŞ ALANI : **73.70 km2** **YAKLAŞIK KOT : 40 m**

GÖZLEM SÜRESİ : **09.11.1979 - 30.09.2006**

ORTALAMA AKIMLAR : **Gözlem süresinde 0.473 m3/sn. (27 Yıllık) 2006 Su yılında 0.699 m3/sn.**

ANLIK EN ÇOK VE EN AZ AKIMLAR:

2006 Su yılında anlık ençok akım	:	**36.0**	**m3/sn**	**08.03.2006**
2006 Su yılında anlık enaz akım	:	**0.000**	**m3/sn**	**01.10.2005**
Gözlem süresinde anlık ençok akım	:	**57.0**	**m3/sn**	**07.12.1997**
Gözlem süresinde anlık enaz akım	:	**0.000**	**m3/sn**	**01.10.1986**

6. Anahtar Eğrisi (Seviyeler cm olarak)

Seviye	Akım	Seviye	Akım	Seviye	Akım	Seviye	Akım
1	0.000	67	6.9	125	19.0	228	40.0
10	0.001	76	8.8	144	23.0	243	45.0
40	2.4	86	10.5	165	27.0	268	49.0
49	3.8	97	13.0	183	31.0	284	54.0
58	5.4	108	16.0	204	36.0		

Akımlar 01 Ekim 2005 'den 30 Eylül 2006' a kadar m3/sn olarak

Gün	Ekim	Kasım	Aralık	Ocak	Şubat	Mart	Nisan	Mayıs	Haziran	Temmuz	Ağustos	Eylül
01	KURU	KURU	1.29	0.552	1.06	1.57	0.700	0.330	0.143	0.143	KURU	KURU
02	KURU	KURU	1.06	0.404	1.43	1.29	0.626	0.282	0.143	0.143	KURU	KURU
03	KURU	KURU	0.970	0.282	1.98	1.15	0.626	0.282	0.143	0.880	KURU	KURU
04	KURU	KURU	0.790	0.282	1.98	0.970	0.626	0.282	0.143	0.282	KURU	KURU
05	KURU	KURU	0.700	0.282	1.98	0.880	0.626	0.233	0.100	0.282	KURU	KURU
06	KURU	KURU	0.626	0.282	7.40	0.790	0.552	0.233	0.100	0.233	KURU	KURU
07	KURU	0.022	0.478	0.282	2.90	3.80	0.552	0.233	0.100	0.233	KURU	KURU
08	KURU	0.074	0.404	0.282	2.26	9.90	0.552	0.233	0.100	0.233	KURU	KURU
09	KURU	0.143	0.330	0.282	1.71	2.90	0.552	0.233	0.626	0.233	KURU	KURU
10	KURU	0.100	0.404	0.282	2.90	2.26	0.552	0.233	1.06	0.185	KURU	KURU
11	0.048	0.100	0.330	0.404	6.40	2.26	0.552	0.233	0.233	0.185	KURU	KURU
12	0.009	0.143	0.282	0.626	2.80	2.26	0.552	0.233	0.233	0.143	KURU	KURU
13	KURU	0.143	0.233	1.06	1.57	1.84	0.478	0.404	0.185	0.100	KURU	KURU
14	KURU	0.143	0.233	0.790	1.06	5.20	0.478	0.282	0.185	0.100	KURU	KURU
15	KURU	0.143	0.185	1.06	0.880	3.80	0.478	0.233	0.185	0.074	KURU	KURU
16	KURU	0.143	0.185	1.29	0.790	3.10	0.404	0.233	0.185	0.048	KURU	KURU
17	KURU	0.185	0.185	0.970	2.60	2.26	0.404	0.233	0.185	0.048	KURU	KURU
18	KURU	0.233	1.15	0.790	14.5	2.26	0.404	0.233	0.185	0.022	KURU	KURU
19	KURU	0.233	2.12	2.80	5.70	2.12	0.404	0.185	0.185	0.022	KURU	KURU
20	KURU	0.478	0.880	2.60	4.80	1.71	0.404	0.185	0.185	0.022	KURU	KURU
21	KURU	0.330	0.626	1.29	3.70	1.43	0.404	0.185	0.185	0.022	KURU	KURU
22	KURU	0.626	0.552	0.970	2.80	1.29	0.330	0.185	0.185	0.022	KURU	KURU
23	KURU	1.57	0.552	1.57	2.26	1.15	0.330	0.185	0.185	0.009	KURU	KURU
24	KURU	2.80	0.478	1.29	2.12	0.970	0.330	0.185	0.143	0.009	KURU	KURU
25	KURU	5.20	0.404	1.15	5.80	0.970	0.330	0.185	0.143	0.003	KURU	KURU
26	KURU	3.50	0.404	1.15	4.80	0.970	0.330	0.143	0.143	0.001	KURU	KURU
27	KURU	2.12	0.404	0.970	2.90	0.880	0.330	0.143	0.143	0.001	KURU	KURU
28	KURU	1.71	0.404	0.880	2.12	0.790	0.330	0.143	0.143	KURU	KURU	KURU
29	KURU	1.43	0.330	0.880	-----	0.700	0.330	0.143	0.143	KURU	KURU	KURU
30	KURU	1.43	0.330	0.880	-----	0.700	0.330	0.143	0.143	KURU	KURU	KURU
31	KURU	-----	0.552	0.880	-----	0.700	-----	0.143	-----	KURU	KURU	-----
Maks.	13.5	16.0	15.0	15.0	32.0	36.0	0.700	1.15	1.84	12.0	KURU	KURU
Min.	KURU	KURU	0.185	0.282	0.626	0.626	0.282	0.143	0.074	KURU	KURU	KURU
Ortalama	0.002	0.767	0.576	0.887	3.33	2.03	0.463	0.220	0.205	0.119	KURU	KURU
LT/SN/Km2	0.025	10.4	7.82	12.0	45.2	27.5	6.28	2.98	2.79	1.61	0.000	0.000
AKIM mm.	0.067	27.0	21.0	32.3	109.	73.7	16.3	7.98	7.22	4.31	0.000	0.000
MİL. M3	0.005	1.99	1.54	2.38	8.05	5.43	1.20	0.588	0.532	0.318	0.000	0.000

SU YILI (2006) YILLIK TOPLAM AKIM 22.03 MİLYON M3 299 MM. 9.5 LT/SN/Km2

02. Marmara Havzasi

D02A070 BAYRAM DERE Adatepe

YERİ : **CANAKKALE-BIGA KARAYOLU 41.NCI KM.SINDE ADATEPE KOYU KOPRUSUNDEDIR.**
26°46'41" Doğu - 40°23'46" Kuzey

YAĞIŞ ALANI : **87.00 km2** **YAKLAŞIK KOT : 18 m**

GÖZLEM SÜRESİ : **07.11.1979 - 30.09.2006**

ORTALAMA AKIMLAR : **Gözlem süresinde 0.482 m3/sn. (25 Yıllık) 2006 Su yılında 1.018 m3/sn.**

ANLIK EN ÇOK VE EN AZ AKIMLAR:

2006 Su yılında anlık ençok akım	:	**84.0**	**m3/sn**	**20.03.2006**
2006 Su yılında anlık enaz akım	:	**0.000**	**m3/sn**	**12.11.2005**
Gözlem süresinde anlık ençok akım	:	**105.**	**m3/sn**	**17.12.1988**
Gözlem süresinde anlık enaz akım	:	**0.000**	**m3/sn**	**25.07.1986**

5. Anahtar Eğrisi (Seviyeler cm olarak)

Seviye	Akım	Seviye	Akım	Seviye	Akım	Seviye	Akım
1	0.000	31	2.2	61	12.0	98	35.0
7	0.010	37	3.5	67	15.0	107	43.0
13	0.190	43	5.0	75	19.0	146	83.0
19	0.510	49	7.0	83	24.0	161	100.
25	1.2	55	9.2	91	30.0		

Akımlar 01 Ekim 2005 'den 30 Eylül 2006' a kadar m3/sn olarak

Gün	Ekim	Kasım	Aralık	Ocak	Şubat	Mart	Nisan	Mayıs	Haziran	Temmuz	Ağustos	Eylül
01	0.007	0.019	0.030	1.89	0.490	1.17	0.590	0.155	0.086	0.059	0.007	KURU
02	0.007	0.019	0.030	1.73	1.32	1.03	0.590	0.155	0.086	0.059	KURU	KURU
03	0.007	0.019	0.030	0.790	1.60	1.03	0.490	0.155	0.086	0.059	KURU	KURU
04	0.007	0.019	0.030	0.410	1.32	0.890	0.490	0.155	0.086	0.059	0.001	KURU
05	0.007	0.019	0.030	0.690	1.60	0.790	0.490	0.155	0.086	0.059	0.001	KURU
06	0.007	0.019	0.030	2.05	4.40	0.690	0.490	0.155	0.086	0.059	KURU	KURU
07	0.019	0.019	0.030	2.05	2.38	0.790	0.490	0.155	0.086	0.030	KURU	KURU
08	0.019	0.019	0.030	0.890	1.73	2.05	0.490	0.155	0.086	0.030	KURU	KURU
09	0.019	0.030	0.030	0.890	0.890	1.46	0.490	0.155	0.086	0.030	KURU	KURU
10	0.019	0.030	0.030	0.490	3.55	1.32	0.490	0.155	0.086	0.030	KURU	KURU
11	0.019	0.030	0.030	0.335	16.6	2.05	0.490	0.155	0.086	0.044	KURU	KURU
12	0.019	0.030	0.030	0.335	31.2	7.00	0.410	0.118	0.086	0.044	KURU	KURU
13	0.019	0.019	0.030	0.335	6.74	3.55	0.410	0.118	0.155	0.059	KURU	KURU
14	0.019	0.019	0.030	0.275	0.890	5.96	0.410	0.118	0.155	0.086	KURU	KURU
15	0.019	0.019	0.059	0.205	0.590	4.40	0.335	0.118	0.155	0.086	KURU	KURU
16	0.019	0.019	0.059	0.205	0.410	4.19	0.335	0.118	0.118	0.030	KURU	KURU
17	0.007	0.019	0.059	0.335	1.17	5.70	0.335	0.118	0.118	0.030	KURU	KURU
18	0.019	0.019	0.059	0.410	5.44	40.8	0.275	0.118	0.118	0.044	KURU	KURU
19	0.019	0.019	0.155	1.46	3.98	61.6	0.275	0.118	0.118	0.044	KURU	KURU
20	0.019	0.019	0.118	2.38	3.05	10.3	0.275	0.086	0.118	0.044	KURU	KURU
21	0.019	0.019	0.118	1.17	3.55	1.46	0.205	0.086	0.118	0.019	KURU	KURU
22	0.019	0.019	0.155	0.890	4.19	1.32	0.205	0.155	0.086	0.019	KURU	KURU
23	0.019	0.019	0.205	1.89	4.19	1.03	0.205	0.155	0.059	0.019	KURU	KURU
24	0.007	0.030	0.155	1.17	4.40	1.03	0.205	0.118	0.059	0.019	KURU	KURU
25	0.019	0.086	0.155	1.17	12.3	0.890	0.205	0.118	0.059	0.030	KURU	KURU
26	0.019	0.030	0.155	1.17	23.5	0.790	0.205	0.118	0.059	0.044	KURU	KURU
27	0.019	0.030	0.275	1.17	7.00	2.72	0.155	0.118	0.059	0.030	KURU	0.030
28	0.019	0.030	0.410	0.690	1.46	1.03	0.155	0.118	0.059	0.030	KURU	0.019
29	0.019	0.030	0.275	0.590	-----	0.790	0.155	0.086	0.059	0.030	KURU	0.030
30	0.019	0.030	0.205	0.690	-----	0.690	0.118	0.086	0.059	0.030	KURU	0.019
31	0.019	-----	0.490	0.490	-----	0.590	-----	0.118	-----	0.019	KURU	-----
Maks.	0.019	0.205	0.890	6.74	52.8	84.0	1.03	0.790	0.155	0.086	0.007	0.044
Min.	0.001	KURU	KURU	0.155	0.410	0.590	0.118	0.059	0.044	0.019	KURU	KURU
Ortalama	0.016	0.025	0.114	0.943	5.36	5.46	0.349	0.129	0.092	0.041	0.000	0.003
LT/SN/Km2	0.183	0.286	1.31	10.8	61.6	62.7	4.01	1.49	1.06	0.472	0.003	0.038
AKIM mm.	0.490	0.742	3.50	29.0	149.	168.	10.4	3.98	2.74	1.27	0.009	0.097
MİL. M3	0.043	0.065	0.305	2.53	13.0	14.6	0.904	0.347	0.239	0.110	0.001	0.008

SU YILI (2006) YILLIK TOPLAM AKIM 32.15 MİLYON M3 370 MM. 11.7 LT/SN/Km2

02. Marmara Havzasi

D02A077 Safran D. Kurtköy

YERİ : 1985Yalova termal yolunun 8 km.şindeki Kadıköy ün içinden geçi-lerek yola devam edilir.5 km sonra köye gelinir.İstasyon kö-
39°13'0" Doğu - 40°34'0" Kuzey

YAĞIŞ ALANI : 51,48 km2 **YAKLAŞIK KOT :** 131 m

GÖZLEM SÜRESİ : 10.07.1980 - 30.09.2006

ORTALAMA AKIMLAR : Gözlem süresinde 0.890 m3/sn. (6 Yıllık) 2006 Su yılında 0.982 m3/sn.

ANLIK EN ÇOK VE EN AZ AKIMLAR:

2006 Su yılında anlık ençok akım	:	8.04	m3/sn	27.02.2006
2006 Su yılında anlık enaz akım	:	0.071	m3/sn	06.10.2005
Gözlem süresinde anlık ençok akım	:	12.5	m3/sn	06.03.1981
Gözlem süresinde anlık enaz akım	:	0.010	m3/sn	28.07.1985

13. Anahtar Eğrisi (Seviyeler cm olarak)

Seviye	Akım	Seviye	Akım	Seviye	Akım	Seviye	Akım
11	0.066	20	0.350	34	1.0	60	2.9
13	0.120	22	0.400	36	1.2	70	3.8
15	0.180	23	0.480	40	1.4	80	4.9
16	0.215	25	0.580	47	1.8	90	6.0
18	0.280	30	0.800	50	2.1	100	7.0

Akımlar 01 Ekim 2005 'den 30 Eylül 2006' a kadar m3/sn olarak

Gün	Ekim	Kasım	Aralık	Ocak	Şubat	Mart	Nisan	Mayıs	Haziran	Temmuz	Ağustos	Eylül
01	0.091	0.250	0.810	1.25	1.35	4.99	1.70	0.810	0.477	0.343	0.176	0.110
02	0.132	0.198	0.770	1.25	1.35	4.72	1.70	0.810	0.477	0.310	0.176	0.132
03	0.132	0.176	0.730	1.25	1.40	5.44	1.58	0.770	0.477	0.310	0.176	0.110
04	0.091	0.198	0.655	1.25	1.46	4.45	1.52	0.770	0.477	0.310	0.176	0.132
05	0.091	0.198	0.620	1.25	1.52	3.86	1.46	0.770	0.440	0.310	0.176	0.132
06	0.071	0.220	0.585	1.25	1.64	3.65	1.40	0.770	0.440	0.310	0.154	0.110
07	0.071	0.280	0.550	1.25	1.52	3.51	1.40	0.770	0.440	0.310	0.176	0.110
08	0.091	0.250	0.585	1.25	1.46	3.58	1.35	0.730	0.477	0.310	0.176	0.110
09	0.071	0.250	0.550	1.25	1.35	3.30	1.30	0.690	0.477	0.280	0.154	0.110
10	0.071	0.250	0.513	1.25	2.24	3.02	1.25	0.690	0.585	0.280	0.154	0.110
11	0.071	0.250	0.513	1.25	4.63	3.30	1.25	0.690	0.477	0.280	0.154	0.110
12	0.091	0.250	0.477	1.25	3.09	4.90	1.20	0.690	0.440	0.250	0.154	0.132
13	0.071	0.250	0.477	1.25	2.74	4.99	1.20	0.655	0.550	0.280	0.132	0.132
14	0.091	0.280	0.477	1.25	2.42	4.72	1.16	0.655	0.477	0.250	0.154	0.132
15	0.091	0.343	0.440	1.25	2.18	4.36	1.11	0.655	0.477	0.250	0.154	0.154
16	0.110	0.343	0.513	1.25	2.06	3.93	1.07	0.655	0.440	0.250	0.132	0.176
17	0.132	0.310	0.550	1.25	1.94	3.58	1.07	0.655	0.408	0.250	0.132	0.176
18	0.110	0.375	0.620	1.25	2.42	3.23	1.02	0.620	0.408	0.220	0.132	0.176
19	0.091	0.408	0.810	1.25	3.16	3.02	1.02	0.620	0.408	0.220	0.110	0.176
20	0.110	0.975	0.730	1.94	3.65	2.88	0.975	0.620	0.375	0.220	0.132	0.176
21	0.091	0.930	0.730	2.36	4.00	2.67	0.975	0.585	0.375	0.198	0.132	0.198
22	0.091	0.730	0.690	2.12	4.00	2.54	0.930	0.585	0.375	0.198	0.110	0.198
23	0.071	0.850	0.690	2.00	4.00	2.54	0.930	0.585	0.343	0.198	0.110	0.198
24	0.071	1.11	0.690	1.82	4.00	2.48	0.930	0.550	0.343	0.198	0.110	0.176
25	0.071	1.70	0.690	1.76	4.63	2.30	0.890	0.550	0.343	0.176	0.110	0.310
26	0.071	2.18	0.730	1.64	6.00	2.18	0.890	0.550	0.343	0.176	0.110	0.220
27	0.071	1.70	0.890	1.52	6.40	2.06	0.890	0.550	0.343	0.198	0.110	0.176
28	0.091	1.30	1.40	1.46	5.26	2.00	0.850	0.513	0.408	0.176	0.110	0.198
29	0.091	1.07	1.25	1.40	-----	1.88	0.850	0.513	0.343	0.176	0.110	0.250
30	0.154	0.930	1.25	1.35	-----	1.88	0.810	0.513	0.343	0.176	0.110	0.220
31	0.440	-----	1.25	1.35	-----	1.76	-----	0.513	-----	0.176	0.110	-----
Maks.	1.25	3.09	1.82	3.23	8.04	7.09	1.76	0.850	0.975	0.375	0.198	0.440
Min.	0.071	0.176	0.440	0.440	1.30	1.76	0.810	0.513	0.310	0.154	0.091	0.091
Ortalama	0.103	0.618	0.717	1.43	2.92	3.35	1.16	0.648	0.426	0.245	0.139	0.162
LT/SN/Km2	2.00	12.0	13.9	27.9	56.8	65.0	22.5	12.6	8.28	4.76	2.70	3.14
AKIM mm.	5.36	31.1	37.3	74.6	137.	174.	58.2	33.7	21.5	12.7	7.24	8.14
MİL. M3	0.276	1.60	1.92	3.84	7.07	8.96	3.00	1.74	1.10	0.656	0.373	0.419

SU YILI (2006) YILLIK TOPLAM AKIM 30.95 MİLYON M3 601 MM. 19.1 LT/SN/Km2

02. Marmara Havzasi

D02A083 KARPUZ D. TESVİKİYE

YERİ : **YALOVA ÇINARCIK NAHİYESİNDEN TEŞVİKİYE KÖYÜNE GELİNİR. İSTASYON KÖYÜN 1.5 KM MANSABINDADIR**

29°4'0" Doğu - 40°37'0" Kuzey

YAĞIŞ ALANI : **46,20 km2** **YAKLAŞIK KOT : 52 m**

GÖZLEM SÜRESİ : **30.04.1984 - 30.09.2006**

ORTALAMA AKIMLAR : **Gözlem süresinde 1.285 m3/sn. (11 Yıllık) 2006 Su yılında 2.265 m3/sn.**

ANLIK EN ÇOK VE EN AZ AKIMLAR:

2006 Su yılında anlık ençok akım	**:**	**62.0**	**m3/sn**	**03.03.2006**
2006 Su yılında anlık enaz akım	**:**	**0.000**	**m3/sn**	**01.10.2005**
Gözlem süresinde anlık ençok akım	**:**	**350.**	**m3/sn**	**03.12.2001**
Gözlem süresinde anlık enaz akım	**:**	**0.000**	**m3/sn**	**07.07.1984**

İstasyon için kullanılmış anahtar bulunamadı.

Akımlar 01 Ekim 2005 'den 30 Eylül 2006' a kadar m3/sn olarak

Gün	Ekim	Kasım	Aralık	Ocak	Şubat	Mart	Nisan	Mayıs	Haziran	Temmuz	Ağustos	Eylül
01	KURU	1.57	1.57	6.40	0.953	27.7	6.40	0.350	KURU	KURU	KURU	KURU
02	KURU	0.560	1.15	2.92	0.953	20.0	5.44	0.560	KURU	KURU	KURU	KURU
03	KURU	0.250	1.36	1.99	1.15	37.0	5.44	0.560	KURU	KURU	KURU	KURU
04	KURU	0.350	1.15	1.78	1.15	19.2	5.92	0.560	KURU	KURU	KURU	KURU
05	KURU	0.757	0.953	1.36	1.36	13.5	5.44	0.560	KURU	KURU	KURU	KURU
06	KURU	0.350	0.757	1.15	1.36	15.8	4.48	0.757	KURU	KURU	KURU	KURU
07	KURU	0.757	0.560	1.15	1.15	18.3	4.00	0.757	KURU	KURU	KURU	KURU
08	KURU	0.560	0.560	1.15	1.78	18.3	4.00	0.560	KURU	KURU	KURU	KURU
09	KURU	0.560	0.757	1.36	1.78	10.7	3.64	0.350	KURU	KURU	KURU	KURU
10	KURU	0.560	0.757	1.15	3.28	7.75	3.28	0.350	KURU	KURU	KURU	KURU
11	KURU	0.560	0.560	0.757	10.7	7.75	2.92	0.350	KURU	KURU	KURU	KURU
12	KURU	0.560	0.560	0.350	6.85	14.3	2.56	0.350	KURU	KURU	KURU	KURU
13	KURU	0.560	0.560	0.350	4.96	14.3	2.56	0.350	KURU	KURU	KURU	KURU
14	KURU	0.757	0.560	0.560	3.64	16.7	2.20	0.350	KURU	KURU	KURU	KURU
15	KURU	2.20	0.560	0.250	3.28	12.0	1.99	0.250	KURU	KURU	KURU	KURU
16	KURU	1.36	0.560	0.140	2.56	8.83	1.78	0.250	KURU	KURU	KURU	KURU
17	0.953	1.15	0.757	0.140	2.20	6.40	1.57	0.250	KURU	KURU	KURU	KURU
18	0.001	1.99	0.953	0.030	5.92	4.48	1.36	0.350	KURU	KURU	KURU	KURU
19	KURU	3.28	1.15	1.57	8.83	4.00	1.15	0.250	KURU	KURU	KURU	KURU
20	KURU	10.1	1.78	1.57	10.1	3.64	0.953	0.140	KURU	KURU	KURU	KURU
21	KURU	6.40	1.36	0.757	10.7	4.00	0.953	0.070	KURU	KURU	KURU	KURU
22	KURU	3.28	1.15	0.757	10.7	6.85	0.953	0.030	KURU	KURU	KURU	KURU
23	KURU	2.20	0.953	0.350	11.4	10.7	0.953	KURU	KURU	KURU	KURU	KURU
24	KURU	4.00	0.560	0.250	10.7	15.0	0.757	KURU	KURU	KURU	KURU	KURU
25	KURU	12.0	0.350	0.350	15.0	9.47	0.757	KURU	KURU	KURU	KURU	KURU
26	KURU	10.7	0.350	0.250	28.8	6.85	0.350	KURU	KURU	KURU	KURU	KURU
27	KURU	6.40	1.15	0.560	28.8	6.40	0.350	KURU	KURU	KURU	KURU	KURU
28	KURU	4.00	3.28	0.350	19.2	5.92	0.350	KURU	KURU	KURU	KURU	KURU
29	KURU	2.92	6.85	0.560	-----	6.85	0.350	KURU	KURU	KURU	KURU	KURU
30	KURU	1.99	5.92	0.560	-----	8.83	0.350	KURU	KURU	KURU	KURU	KURU
31	1.36	-----	11.4	0.757	-----	6.85	-----	KURU	-----	KURU	KURU	-----
Maks.	2.56	23.3	21.1	9.47	37.0	62.0	7.30	0.757	0.070	KURU	KURU	KURU
Min.	KURU	0.250	0.250	0.001	0.953	3.64	0.350	KURU	KURU	KURU	KURU	KURU
Ortalama	0.075	2.76	1.64	1.02	7.47	11.9	2.44	0.269	KURU	KURU	KURU	KURU
LT/SN/Km2	1.62	59.7	35.5	22.1	162.	257.	52.8	5.83	0.000	0.000	0.000	0.000
AKIM mm.	4.33	155.	95.2	59.1	391.	689.	137.	15.6	0.000	0.000	0.000	0.000
MİL. M3	0.200	7.14	4.40	2.73	18.1	31.8	6.32	0.722	0.000	0.000	0.000	0.000

SU YILI (2006) YILLIK TOPLAM AKIM 71.41 MİLYON M3 1546 MM. 49.0 LT/SN/Km2

02. Marmara Havzasi

D02A084 Kocaçay Aşağıçavuş

YERİ : **ASAGICAVUS KOYUNÜN 1.5 KM. BATISINDAKİ KÖPRÜDEDIR.**
27°5'58" Doğu - 39°49'2" Kuzey

YAĞIŞ ALANI : **51.80 km2** **YAKLAŞIK KOT : 295 m**

GÖZLEM SÜRESİ : **01.10.1984 - 30.09.2006**

ORTALAMA AKIMLAR : **Gözlem süresinde 0.978 m3/sn. (22 Yıllık) 2006 Su yılında 1.414 m3/sn.**

ANLIK EN ÇOK VE EN AZ AKIMLAR:

2006 Su yılında anlık ençok akım	**:**	**57.0**	**m3/sn**	**25.11.2005**
2006 Su yılında anlık enaz akım	**:**	**0.130**	**m3/sn**	**01.10.2005**
Gözlem süresinde anlık ençok akım	**:**	**76.0**	**m3/sn**	**06.03.2005**
Gözlem süresinde anlık enaz akım	**:**	**0.082**	**m3/sn**	**31.08.2003**

4. Anahtar Eğrisi (Seviyeler cm olarak)

Seviye	Akım	Seviye	Akım	Seviye	Akım	Seviye	Akım
3	0.012	78	9.1	120	19.5	190	40.0
12	0.113	86	11.0	134	23.0	203	43.0
28	0.616	95	13.0	147	27.0	218	47.0
62	5.8	104	15.0	164	31.0	231	51.0
70	7.4	112	17.0	176	35.0	244	55.0

Akımlar 01 Ekim 2005 'den 30 Eylül 2006' a kadar m3/sn olarak

Gün	Ekim	Kasım	Aralık	Ocak	Şubat	Mart	Nisan	Mayıs	Haziran	Temmuz	Ağustos	Eylül
01	0.146	0.185	0.294	3.98	0.980	11.0	2.45	1.14	0.658	0.370	0.183	0.207
02	0.447	0.185	0.294	3.11	0.980	7.40	2.28	1.14	0.658	0.411	0.183	0.183
03	0.420	0.185	0.294	2.61	0.980	7.60	2.28	1.06	0.658	0.447	0.183	0.183
04	0.162	0.185	0.294	2.12	0.980	6.20	2.28	1.06	0.658	0.411	0.183	0.183
05	0.162	0.185	0.258	1.95	1.06	5.30	2.12	1.06	0.658	0.370	0.183	0.183
06	0.146	0.185	0.258	1.72	1.61	4.73	1.95	0.980	0.591	0.329	0.183	0.183
07	0.146	0.185	0.258	1.61	1.30	8.70	1.95	0.980	0.591	0.329	0.183	0.183
08	0.146	0.185	0.294	1.49	1.30	11.6	1.95	0.980	0.591	0.329	0.183	0.183
09	0.146	0.185	0.329	1.30	1.14	7.20	1.84	0.980	0.591	0.302	0.159	0.183
10	0.146	0.185	0.375	1.30	1.38	6.00	1.72	0.907	0.591	0.302	0.183	0.183
11	0.162	0.185	0.420	1.22	1.84	9.10	1.72	0.907	0.591	0.302	0.183	0.183
12	0.185	0.185	0.447	1.14	1.72	12.6	1.72	0.907	0.591	0.275	0.183	0.183
13	0.185	0.185	0.447	1.06	1.61	9.30	1.72	0.907	0.591	0.275	0.183	0.183
14	0.162	0.185	0.447	1.06	1.49	8.30	1.72	0.834	0.537	0.241	0.183	0.183
15	0.162	0.185	0.420	0.980	1.30	7.20	1.61	0.834	0.537	0.241	0.183	0.183
16	0.162	0.185	0.375	0.980	1.49	6.40	1.61	0.834	0.537	0.241	0.183	0.183
17	0.162	0.294	0.329	0.980	1.84	5.50	1.61	0.834	0.483	0.241	0.183	0.183
18	0.162	0.420	3.51	0.907	3.27	4.92	1.61	0.779	0.483	0.241	0.183	0.183
19	0.162	0.375	2.61	1.61	3.98	4.36	1.61	0.779	0.447	0.207	0.183	0.183
20	0.162	0.375	1.06	1.72	6.00	3.98	1.61	0.779	0.447	0.207	0.183	0.183
21	0.162	0.329	0.837	1.38	4.73	3.27	1.61	0.779	0.447	0.207	0.183	0.183
22	0.162	0.294	0.635	1.30	4.17	3.11	1.49	0.779	0.447	0.207	0.183	0.207
23	0.162	0.375	0.568	1.49	3.60	2.78	1.49	0.779	0.411	0.207	0.183	0.207
24	0.162	3.32	0.568	1.30	3.60	3.27	1.38	0.779	0.411	0.207	0.183	0.411
25	0.162	17.6	0.521	1.30	10.0	3.11	1.38	0.779	0.411	0.207	0.183	0.370
26	0.162	1.74	0.521	1.14	12.6	2.78	1.38	0.724	0.411	0.207	0.183	0.329
27	0.162	1.30	0.702	1.06	12.3	2.61	1.38	0.658	0.411	0.207	0.183	0.329
28	0.162	0.635	2.61	0.980	10.0	2.45	1.30	0.658	0.411	0.207	0.183	0.302
29	0.162	0.474	11.0	0.980	-----	2.28	1.14	0.658	0.411	0.207	0.183	1.14
30	0.207	0.375	7.60	0.980	-----	2.28	1.14	0.658	0.411	0.207	0.183	0.537
31	0.185	-----	5.70	0.980	-----	2.12	-----	0.658	-----	0.207	0.183	-----
Maks.	1.22	57.0	17.9	5.11	22.8	22.1	2.45	1.14	0.779	0.447	0.302	8.50
Min.	0.130	0.185	0.258	0.907	0.980	2.12	1.14	0.658	0.370	0.207	0.159	0.159
Ortalama	0.180	1.03	1.43	1.48	3.47	5.72	1.70	0.858	0.522	0.269	0.182	0.257
LT/SN/Km2	3.48	19.9	27.6	28.5	67.1	111.	32.9	16.6	10.1	5.20	3.52	4.95
AKIM mm.	9.31	51.5	73.8	76.3	162.	296.	85.1	44.4	26.1	13.9	9.42	12.8
MİL. M3	0.482	2.67	3.83	3.95	8.40	15.3	4.41	2.30	1.35	0.721	0.488	0.665

SU YILI (2006) YILLIK TOPLAM AKIM 44.57 MİLYON M3 860 MM. 27.3 LT/SN/Km2

02. Marmara Havzasi

D02A085 KOCABAS ÇAYI Uzunalan

YERİ : **ÇAN-UZUNALAN KOYU ETILER BELDE YOLU UZERINDE KOPRUDEDIR.**
26°56'42" Doğu - 39°57'8" Kuzey

YAĞIŞ ALANI : **165.00 km2** **YAKLAŞIK KOT : 141 m**

GÖZLEM SÜRESİ : **01.10.1984 - 30.09.2006**

ORTALAMA AKIMLAR : **Gözlem süresinde 1.364 m3/sn. (19 Yıllık) 2006 Su yılında 2.191 m3/sn.**

ANLIK EN ÇOK VE EN AZ AKIMLAR:

2006 Su yılında anlık ençok akım	:	**32.3**	**m3/sn**	**18.02.2006**
2006 Su yılında anlık enaz akım	:	**0.016**	**m3/sn**	**31.07.2006**
Gözlem süresinde anlık ençok akım	:	**210.**	**m3/sn**	**05.10.1991**
Gözlem süresinde anlık enaz akım	:	**0.000**	**m3/sn**	**20.07.1985**

9. Anahtar Eğrisi (Seviyeler cm olarak)

Seviye	Akım	Seviye	Akım	Seviye	Akım	Seviye	Akım
20	0.000	140	35.0	263	125.	336	185.
30	0.016	190	68.0	277	135.	350	200.
40	0.220	225	96.0	293	150.	380	220.
60	2.2	231	100.	307	160.		
92	11.0	247	110.	318	175.		

Akımlar 01 Ekim 2005 'den 30 Eylül 2006' a kadar m3/sn olarak

Gün	Ekim	Kasım	Aralık	Ocak	Şubat	Mart	Nisan	Mayıs	Haziran	Temmuz	Ağustos	Eylül
01	0.055	0.187	3.00	3.40	1.93	13.5	2.07	0.890	0.220	0.153	0.095	0.055
02	0.320	0.153	2.40	2.60	2.07	9.67	1.93	0.890	0.220	0.120	0.095	0.040
03	0.220	0.153	2.07	2.20	1.80	9.67	1.80	0.890	0.220	0.220	0.095	0.040
04	0.153	0.153	1.67	2.07	2.07	8.00	1.80	0.800	0.187	0.187	0.095	0.040
05	0.120	0.153	1.53	1.93	2.20	7.00	1.80	0.710	0.187	0.220	0.070	0.040
06	0.120	0.153	1.30	1.93	7.33	6.40	1.53	0.710	0.187	0.220	0.070	0.040
07	0.095	0.153	1.19	1.80	5.00	10.3	1.53	0.710	0.220	0.187	0.070	0.040
08	0.095	0.153	1.19	1.80	5.53	18.5	1.53	0.800	0.270	0.187	0.070	0.040
09	0.095	0.153	1.53	1.67	5.53	12.2	1.53	0.800	0.800	0.120	0.070	0.040
10	0.095	0.153	1.30	1.67	8.33	7.00	1.40	0.710	0.800	0.120	0.055	0.040
11	0.120	0.153	1.19	1.93	20.5	8.00	1.40	0.620	0.710	0.120	0.055	0.055
12	0.220	0.153	1.19	2.60	11.8	11.0	1.30	0.710	0.710	0.153	0.055	0.055
13	0.153	0.153	1.09	3.60	8.67	8.33	1.30	0.800	0.710	0.153	0.055	0.055
14	0.153	0.153	1.09	2.80	7.33	11.0	1.19	0.710	0.710	0.120	0.055	0.055
15	0.120	0.153	0.980	2.80	6.40	9.00	1.19	0.710	0.530	0.120	0.055	0.055
16	0.153	0.153	0.980	3.20	5.80	7.00	1.09	0.620	0.710	0.120	0.055	0.055
17	0.153	0.153	0.980	3.20	7.33	5.53	1.09	0.620	0.530	0.095	0.055	0.055
18	0.120	0.270	2.07	3.00	19.0	6.70	1.09	0.530	0.380	0.095	0.040	0.070
19	0.120	0.220	6.70	7.67	17.6	6.70	1.09	0.620	0.320	0.095	0.040	0.095
20	0.120	0.320	3.60	5.00	19.0	5.53	0.980	0.530	0.320	0.095	0.040	0.153
21	0.120	0.320	2.60	2.80	15.2	4.47	1.09	0.530	0.270	0.095	0.040	0.187
22	0.120	0.220	2.20	2.20	13.5	4.00	0.980	0.440	0.270	0.095	0.040	0.153
23	0.120	0.380	1.93	4.20	11.8	3.60	0.980	0.440	0.270	0.095	0.040	0.187
24	0.120	5.00	1.80	3.00	11.4	4.73	0.890	0.380	0.187	0.095	0.040	0.890
25	0.120	18.5	1.53	2.20	20.0	4.20	0.890	0.380	0.187	0.095	0.040	0.890
26	0.095	15.7	1.53	2.07	16.7	3.60	0.890	0.380	0.187	0.120	0.040	0.380
27	0.095	11.0	1.53	1.80	13.1	3.20	0.800	0.380	0.187	0.120	0.055	0.320
28	0.095	8.33	1.80	1.53	10.7	2.80	0.800	0.320	0.187	0.120	0.055	0.270
29	0.120	6.10	2.80	1.53	-----	2.80	0.800	0.270	0.153	0.120	0.055	0.980
30	0.187	4.20	6.10	1.53	-----	2.40	0.800	0.220	0.153	0.095	0.040	0.890
31	0.187	-----	4.47	1.80	-----	2.20	-----	0.187	-----	0.095	0.040	-----
Maks.	0.800	18.5	9.67	21.0	32.3	18.5	2.60	1.19	2.07	0.270	0.095	3.40
Min.	0.040	0.153	0.980	1.53	1.67	2.20	0.800	0.187	0.055	0.016	0.031	0.031
Ortalama	0.135	2.44	2.11	2.63	9.92	7.07	1.25	0.591	0.366	0.130	0.057	0.209
LT/SN/Km2	0.817	14.8	12.8	15.9	60.1	42.8	7.59	3.58	2.22	0.791	0.347	1.27
AKIM mm.	2.19	38.3	34.2	42.7	145.	115.	19.7	9.59	5.76	2.12	0.929	3.28
MİL. M3	0.361	6.32	5.65	7.04	24.0	18.9	3.25	1.58	0.950	0.349	0.153	0.541

SU YILI (2006) YILLIK TOPLAM AKIM 69.09 MİLYON M3 419 MM. 13.3 LT/SN/Km2

02. Marmara Havzasi

D02A092 YAMANDERE KAPAKLI

YERİ : **GEMLİK -ARMUTLU KARAYOLUNUN GEMLIKTEN ITIBAREN 20 KM.SINDEBULUNAN KAPAKLI KÖYÜ KARAYOLU KÖPRÜSÜNÜN 50M MANSABINDADIR.**
28°58'10" Doğu - 40°28'26" Kuzey

YAĞIŞ ALANI : **32,00 km2** **YAKLAŞIK KOT : 6 m**

GÖZLEM SÜRESİ : **01.10.1986 - 30.09.2006**

ORTALAMA AKIMLAR : **Gözlem süresinde 0.358 m3/sn. (14 Yıllık) 2006 Su yılında 0.510 m3/sn.**

ANLIK EN ÇOK VE EN AZ AKIMLAR:

2006 Su yılında anlık ençok akım	:	**9.68**	**m3/sn**	**31.12.2005**
2006 Su yılında anlık enaz akım	:	**0.000**	**m3/sn**	**14.07.2006**
Gözlem süresinde anlık ençok akım	:	**60.0**	**m3/sn**	**09.04.1991**
Gözlem süresinde anlık enaz akım	:	**0.000**	**m3/sn**	**01.10.1986**

İstasyon için kullanılmış anahtar bulunamadı.

Akımlar 01 Ekim 2005 'den 30 Eylül 2006' a kadar m3/sn olarak

Gün	Ekim	Kasım	Aralık	Ocak	Şubat	Mart	Nisan	Mayıs	Haziran	Temmuz	Ağustos	Eylül
01	0.011	0.250	0.250	2.67	0.540	4.60	0.390	0.100	0.044	0.005	KURU	KURU
02	0.011	0.070	0.140	1.33	0.720	3.18	0.320	0.100	0.044	0.005	KURU	KURU
03	0.024	0.070	0.250	0.900	0.720	4.84	0.320	0.100	0.024	0.005	KURU	KURU
04	0.024	0.100	0.140	0.720	0.810	2.80	0.250	0.100	0.024	0.005	KURU	KURU
05	0.024	0.140	0.140	0.540	0.810	1.90	0.250	0.100	0.024	0.005	KURU	KURU
06	0.024	0.070	0.100	0.465	0.900	2.16	0.250	0.100	0.011	0.005	KURU	KURU
07	0.024	0.100	0.100	0.320	0.720	2.41	0.250	0.100	0.011	0.005	KURU	KURU
08	0.024	0.070	0.100	0.320	0.720	2.41	0.195	0.100	0.011	0.005	KURU	KURU
09	0.024	0.070	0.195	0.540	0.540	1.44	0.250	0.100	0.011	0.005	KURU	KURU
10	0.024	0.044	0.100	0.540	2.16	1.23	0.195	0.100	0.011	0.005	KURU	KURU
11	0.024	0.044	0.070	0.465	6.73	1.44	0.195	0.100	0.011	0.005	KURU	KURU
12	0.024	0.044	0.070	0.465	3.30	3.30	0.140	0.070	0.011	0.005	KURU	KURU
13	0.024	0.044	0.070	0.540	1.90	2.93	0.140	0.044	0.011	0.005	KURU	KURU
14	0.024	0.044	0.070	0.465	1.23	2.80	0.140	0.044	0.011	KURU	KURU	KURU
15	0.024	0.070	0.070	0.390	0.900	1.90	0.140	0.044	0.011	KURU	KURU	KURU
16	0.024	0.070	0.100	0.390	0.720	1.33	0.140	0.044	0.011	KURU	KURU	KURU
17	0.024	0.044	0.250	0.320	0.630	1.12	0.140	0.044	0.011	KURU	KURU	KURU
18	0.024	0.390	0.390	0.320	1.67	0.900	0.140	0.044	0.011	KURU	KURU	KURU
19	0.024	0.540	1.23	0.810	3.05	0.810	0.140	0.044	0.011	KURU	KURU	KURU
20	0.024	1.44	0.720	1.55	3.69	0.720	0.100	0.044	0.011	KURU	KURU	KURU
21	0.024	0.900	0.465	0.900	3.43	0.720	0.100	0.044	0.011	KURU	KURU	KURU
22	0.024	0.465	0.320	0.720	3.43	0.810	0.100	0.044	0.011	KURU	KURU	KURU
23	0.024	0.630	0.320	0.540	3.30	0.900	0.100	0.044	0.011	KURU	KURU	KURU
24	0.024	2.03	0.320	0.465	3.05	1.12	0.100	0.044	0.011	KURU	KURU	KURU
25	0.024	3.82	0.250	0.465	4.47	0.720	0.100	0.044	0.011	KURU	KURU	KURU
26	0.024	3.82	0.250	0.390	5.56	0.540	0.100	0.044	0.005	KURU	KURU	KURU
27	0.024	1.67	0.630	0.540	5.44	0.465	0.100	0.044	0.005	KURU	KURU	KURU
28	0.024	0.900	3.18	0.540	3.56	0.390	0.100	0.044	0.005	KURU	KURU	KURU
29	0.024	0.540	4.34	0.465	-----	0.390	0.100	0.044	0.005	KURU	KURU	KURU
30	0.024	0.320	2.93	0.540	-----	0.390	0.100	0.044	0.005	KURU	KURU	KURU
31	0.320	-----	5.32	0.465	-----	0.390	-----	0.044	-----	KURU	KURU	-----
Maks.	0.540	7.70	9.68	4.21	9.40	7.60	0.390	0.100	0.044	0.005	KURU	KURU
Min.	0.011	0.044	0.070	0.250	0.540	0.320	0.100	0.044	0.005	KURU	KURU	KURU
Ortalama	0.033	0.627	0.738	0.648	2.31	1.65	0.169	0.065	0.014	0.002	KURU	KURU
LT/SN/Km2	1.02	19.6	23.1	20.3	72.2	51.5	5.30	2.02	0.422	0.066	0.000	0.000
AKIM mm.	2.74	50.8	61.8	54.2	175.	138.	13.7	5.42	1.09	0.176	0.000	0.000
MİL. M3	0.088	1.63	1.98	1.74	5.59	4.41	0.439	0.173	0.035	0.006	0.000	0.000

SU YILI (2006) YILLIK TOPLAM AKIM 16.09 MİLYON M3 503 MM. 15.9 LT/SN/Km2

02. Marmara Havzasi

D02A094 ISIKLAR D. NAİPKÖY

YERİ : **TEKIRDAG NAIPLER ISIKLAR YOLUNUN 1 KM.SINDEDIR. G18B2**
27°24'0" Doğu - 40°52'0" Kuzey

YAĞIŞ ALANI : **47,00 km2** **YAKLAŞIK KOT : 22 m**

GÖZLEM SÜRESİ : **22.10.1986 - 30.09.2006**

ORTALAMA AKIMLAR : **Gözlem süresinde 0.491 m3/sn. (20 Yıllık) 2006 Su yılında 0.945 m3/sn.**

ANLIK EN ÇOK VE EN AZ AKIMLAR:

2006 Su yılında anlık ençok akım	**:**	**47.0**	**m3/sn**	**24.09.2006**
2006 Su yılında anlık enaz akım	**:**	**0.000**	**m3/sn**	**29.07.2006**
Gözlem süresinde anlık ençok akım	**:**	**135.**	**m3/sn**	**15.10.1997**
Gözlem süresinde anlık enaz akım	**:**	**0.000**	**m3/sn**	**01.07.1990**

İstasyon için kullanılmış anahtar bulunamadı.

Akımlar 01 Ekim 2005 'den 30 Eylül 2006' a kadar m3/sn olarak

Gün	Ekim	Kasım	Aralık	Ocak	Şubat	Mart	Nisan	Mayıs	Haziran	Temmuz	Ağustos	Eylül
01	0.047	0.161	0.131	1.35	0.721	2.81	1.72	0.433	0.233	0.433	0.131	0.375
02	0.433	0.192	0.100	0.913	0.804	2.47	1.60	0.433	0.275	0.638	0.100	0.501
03	0.161	0.192	0.192	0.721	0.721	3.48	1.47	0.433	0.233	0.501	0.047	0.433
04	0.131	0.192	0.131	0.638	0.721	2.98	1.47	0.433	0.192	0.501	0.013	0.161
05	0.100	0.192	0.100	0.570	0.804	2.81	1.35	0.375	0.192	0.638	0.026	0.131
06	0.079	0.192	0.100	0.570	0.913	2.64	1.35	0.375	0.192	0.433	0.192	0.100
07	0.100	0.192	0.079	0.501	0.913	3.85	1.24	0.316	0.233	0.375	0.192	0.047
08	0.131	0.192	0.161	0.433	0.804	5.60	1.35	0.375	0.275	0.375	0.433	0.100
09	0.131	0.192	0.161	0.433	0.804	4.63	1.35	0.316	0.433	0.275	0.233	0.100
10	0.131	0.233	0.131	0.433	2.14	4.82	1.13	0.316	0.316	0.275	0.079	0.233
11	0.131	0.233	0.100	0.375	3.85	6.20	1.02	0.375	0.275	0.316	0.079	0.131
12	0.233	0.233	0.100	0.433	2.98	16.0	1.02	0.375	0.275	0.275	0.131	0.275
13	0.161	0.275	0.100	0.375	2.64	7.40	0.913	0.316	0.275	0.233	0.433	0.057
14	0.161	0.233	0.079	0.375	2.31	8.80	0.804	0.275	0.233	0.233	0.316	0.433
15	0.161	0.233	0.100	0.316	1.97	7.20	0.804	0.275	0.275	0.192	0.375	0.375
16	0.161	0.275	0.161	0.316	1.72	7.40	0.804	0.233	0.501	0.275	0.375	0.316
17	0.161	0.316	0.192	0.501	4.24	6.20	0.721	0.233	0.316	0.275	0.233	0.057
18	0.131	0.433	2.31	0.433	8.56	5.41	0.721	0.233	0.233	0.161	0.100	0.501
19	0.131	0.638	1.72	0.804	5.21	4.63	0.721	0.192	0.192	0.192	0.026	0.433
20	0.131	0.638	0.913	1.13	4.04	4.04	0.638	0.192	0.192	0.192	0.047	0.501
21	0.131	0.375	0.638	0.804	2.98	3.65	0.638	0.161	0.161	0.079	0.100	1.97
22	0.131	0.316	0.570	0.721	2.47	3.31	0.570	0.192	0.131	0.047	0.026	0.233
23	0.131	0.721	0.501	0.804	2.14	2.98	0.570	0.275	0.131	0.047	0.079	0.316
24	0.131	1.24	0.433	0.638	2.31	2.81	0.501	0.275	0.192	0.036	0.192	4.04
25	0.161	6.80	0.501	0.638	3.65	2.47	0.501	0.275	0.501	0.057	0.100	0.638
26	0.131	1.85	1.35	0.570	3.65	2.31	0.501	0.275	0.570	0.079	0.100	0.275
27	0.161	0.638	2.47	0.570	4.63	2.14	0.501	0.275	0.433	0.057	0.079	0.233
28	0.161	0.375	2.31	0.570	3.15	1.97	0.501	0.275	0.501	0.036	0.316	0.433
29	0.161	0.316	1.47	0.501	-----	1.97	0.501	0.275	0.501	0.020	0.433	1.72
30	0.161	0.161	1.02	0.570	-----	1.97	0.501	0.275	0.501	0.036	0.433	0.501
31	0.161	-----	1.85	0.721	-----	1.85	-----	0.233	-----	0.079	0.433	-----
Maks.	3.31	15.0	9.04	1.97	10.0	36.7	1.85	0.501	6.60	3.48	0.570	47.0
Min.	0.007	0.100	0.057	0.316	0.638	1.72	0.375	0.131	0.079	KURU	KURU	KURU
Ortalama	0.149	0.608	0.651	0.604	2.57	4.41	0.916	0.300	0.299	0.237	0.189	0.521
LT/SN/Km2	3.18	12.9	13.8	12.9	54.6	93.9	19.5	6.38	6.36	5.05	4.02	11.1
AKIM mm.	8.51	33.5	37.1	34.4	132.	251.	50.5	17.1	16.5	13.5	10.8	28.7
MİL. M3	0.400	1.57	1.74	1.62	6.21	11.8	2.37	0.803	0.774	0.636	0.506	1.35

SU YILI (2006) YILLIK TOPLAM AKIM 29.78 MİLYON M3 634 MM. 20.1 LT/SN/Km2

02. Marmara Havzasi

D02A098 YULAFLI D. ALAYBEY

YERİ : **KOCAELİ İLÇESİ, KANDIRA - KEFKEN YOLUNUNDAN 3.5 KM GİDİLİR. KARAYOLU KÖPRÜSÜNÜN 100 M. MANSABINDADIR. PAFTA 25.000: EREĞ-F24-D3 30°10'31" Doğu - 41°5'28" Kuzey**

YAĞIŞ ALANI : **209,30 km2** **YAKLAŞIK KOT : 13 m**

GÖZLEM SÜRESİ : **16.05.1989 - 30.09.2006**

ORTALAMA AKIMLAR : **Gözlem süresinde 2.267 m3/sn. (17 Yıllık) 2006 Su yılında 2.753 m3/sn.**

ANLIK EN ÇOK VE EN AZ AKIMLAR:

2006 Su yılında anlık ençok akım	:	**44.2**	**m3/sn**	**11.02.2006**
2006 Su yılında anlık enaz akım	:	**0.000**	**m3/sn**	**27.07.2006**
Gözlem süresinde anlık ençok akım	:	**52.5**	**m3/sn**	**26.11.1989**
Gözlem süresinde anlık enaz akım	:	**0.000**	**m3/sn**	**26.07.1990**

2. Anahtar Eğrisi (Seviyeler cm olarak)

Seviye	Akım	Seviye	Akım	Seviye	Akım	Seviye	Akım
12	0.000	40	1.6	220	18.7	420	47.5
16	0.006	60	3.5	260	23.7	430	49.0
20	0.054	100	7.5	300	29.5	440	50.5
24	0.220	140	11.2	340	35.5	450	52.0
28	0.480	180	14.8	380	41.5	460	53.5

Akımlar 01 Ekim 2005 'den 30 Eylül 2006' a kadar m3/sn olarak

Gün	Ekim	Kasım	Aralık	Ocak	Şubat	Mart	Nisan	Mayıs	Haziran	Temmuz	Ağustos	Eylül
01	0.021	8.54	2.66	3.15	4.72	5.21	1.68	0.716	0.054	0.054	KURU	0.006
02	0.021	1.29	2.46	2.66	6.48	3.93	1.68	0.620	0.034	0.054	KURU	0.021
03	0.054	1.00	5.21	2.46	8.05	12.1	1.68	0.620	0.034	0.034	0.006	0.126
04	0.034	6.77	2.95	2.36	7.95	6.09	1.68	0.620	0.054	0.126	0.003	0.054
05	0.021	5.89	2.76	2.17	7.66	4.13	1.58	0.620	0.034	0.220	0.002	0.054
06	0.021	3.54	2.56	2.07	25.2	3.44	1.58	0.620	0.034	0.165	0.003	0.034
07	0.021	2.07	2.07	2.17	14.3	3.74	1.58	0.540	0.034	0.165	0.021	0.034
08	0.021	1.68	1.97	3.83	15.2	13.0	1.58	0.620	0.165	0.126	0.021	0.086
09	0.021	1.39	2.27	7.56	15.2	24.0	1.58	0.540	0.126	0.165	0.012	0.340
10	0.021	1.20	1.97	3.64	20.4	10.7	1.58	0.480	0.270	0.165	0.006	0.126
11	0.021	1.10	2.07	3.34	36.0	9.32	1.58	0.480	0.340	0.165	0.006	0.054
12	0.021	1.00	2.17	3.05	15.9	9.51	1.58	0.480	0.270	0.165	0.006	0.054
13	0.021	1.39	2.46	3.74	13.7	5.89	1.48	0.540	0.270	0.165	0.006	0.034
14	0.021	4.52	2.36	3.34	10.5	5.01	1.48	0.480	0.620	0.165	0.006	0.034
15	0.021	6.48	2.27	2.66	8.73	7.95	1.48	0.480	0.480	0.126	0.006	0.054
16	0.086	1.68	2.46	2.46	7.56	4.32	1.39	0.400	0.340	0.054	0.006	0.034
17	0.126	1.29	3.64	2.27	9.68	3.83	1.39	0.400	0.340	0.012	0.003	0.021
18	0.086	1.48	3.25	2.27	27.7	3.44	1.29	0.400	0.270	0.003	0.003	0.021
19	0.054	3.05	27.6	4.42	21.9	4.23	1.20	0.340	0.270	0.002	0.002	0.021
20	0.086	12.2	12.8	13.7	18.2	3.15	1.10	0.340	0.220	0.003	0.001	0.034
21	0.054	32.1	5.70	6.58	11.7	2.95	1.10	0.340	0.220	0.054	KURU	0.086
22	0.054	5.50	3.83	4.72	8.24	2.76	1.10	0.220	0.220	0.034	KURU	0.086
23	0.054	2.85	7.46	4.42	6.38	1.87	1.00	0.165	0.165	0.012	KURU	0.054
24	0.054	10.3	8.83	4.13	5.11	1.87	1.00	0.165	0.126	0.006	KURU	0.054
25	0.054	5.60	7.07	4.42	4.62	1.78	1.00	0.126	0.086	0.006	KURU	0.340
26	0.054	4.81	9.32	5.79	8.83	1.68	0.908	0.126	0.086	0.006	KURU	0.165
27	0.054	3.44	7.36	5.40	6.48	1.68	0.908	0.126	0.086	0.002	KURU	0.086
28	0.054	2.17	5.40	5.11	5.70	1.58	0.908	0.126	0.086	KURU	KURU	0.086
29	0.054	4.32	4.13	5.01	-----	1.58	0.908	0.086	0.054	KURU	KURU	0.126
30	0.400	3.34	3.25	4.42	-----	1.58	0.908	0.086	0.054	KURU	0.003	0.165
31	1.48	-----	3.54	4.23	-----	1.68	-----	0.054	-----	KURU	0.003	-----
Maks.	7.36	42.7	41.7	22.3	44.2	31.3	1.78	0.908	1.00	0.270	0.034	1.10
Min.	0.021	0.908	1.87	2.07	4.32	1.58	0.908	0.034	0.034	KURU	KURU	0.006
Ortalama	0.102	4.73	4.96	4.11	12.6	5.29	1.33	0.386	0.181	0.073	0.004	0.083
LT/SN/Km2	0.488	22.6	23.7	19.7	60.1	25.3	6.36	1.84	0.867	0.347	0.019	0.397
AKIM mm.	1.31	58.6	63.5	52.7	145.	67.7	16.5	4.94	2.25	0.930	0.052	1.03
MİL. M3	0.273	12.3	13.3	11.0	30.4	14.2	3.45	1.03	0.470	0.195	0.011	0.215

SU YILI (2006) YILLIK TOPLAM AKIM 86.84 MİLYON M3 415 MM. 13.2 LT/SN/Km2

02. Marmara Havzasi

D02A099 YENİDÜZ D. KANDIRA

YERİ : **KANDIRA İLÇESİNDEKİ KÜÇÜK SANAYİ'NİN KARŞINDADIR. PAFTA: 25.000 EREĞ-F24-D4**
30°8'47" Doğu - 41°4'3" Kuzey

YAĞIŞ ALANI : **120,00 km2** **YAKLAŞIK KOT : 25 m**

GÖZLEM SÜRESİ : **16.05.1989 - 30.09.2006**

ORTALAMA AKIMLAR : **Gözlem süresinde 2.035 m3/sn. (17 Yıllık) 2006 Su yılında 2.800 m3/sn.**

ANLIK EN ÇOK VE EN AZ AKIMLAR:

2006 Su yılında anlık ençok akım	:	**91.0**	**m3/sn**	**01.11.2005**
2006 Su yılında anlık enaz akım	:	**0.000**	**m3/sn**	**29.07.2006**
Gözlem süresinde anlık ençok akım	:	**308.**	**m3/sn**	**20.08.2001**
Gözlem süresinde anlık enaz akım	:	**0.000**	**m3/sn**	**19.07.1990**

3. Anahtar Eğrisi (Seviyeler cm olarak)

Seviye	Akım	Seviye	Akım	Seviye	Akım	Seviye	Akım
8	0.000	23	0.980	110	24.0	260	156.
11	0.011	26	1.4	140	39.0	290	201.
14	0.140	29	1.8	170	59.0	320	252.
17	0.380	50	6.5	200	86.0	350	308.
20	0.660	80	13.5	230	117.		

Akımlar 01 Ekim 2005 'den 30 Eylül 2006' a kadar m3/sn olarak

Gün	Ekim	Kasım	Aralık	Ocak	Şubat	Mart	Nisan	Mayıs	Haziran	Temmuz	Ağustos	Eylül
01	0.011	36.0	1.90	2.59	4.66	5.81	0.860	0.380	0.040	0.011	KURU	KURU
02	0.011	2.13	1.60	1.90	6.04	3.74	0.860	0.380	0.040	0.011	KURU	KURU
03	0.011	0.980	6.27	1.90	7.10	13.8	0.860	0.290	0.040	0.011	KURU	0.001
04	0.011	8.50	3.05	1.60	6.90	5.12	0.860	0.290	0.011	0.011	KURU	0.002
05	0.011	7.70	2.82	1.50	6.27	3.28	0.760	0.290	0.011	0.011	KURU	0.001
06	0.011	3.28	1.75	1.50	23.2	2.59	0.760	0.290	0.011	0.011	KURU	0.001
07	0.011	1.60	1.50	1.60	10.5	3.74	0.760	0.290	0.011	0.011	0.002	0.001
08	0.011	1.10	1.35	5.35	11.3	13.5	0.760	0.290	0.011	0.011	0.002	0.001
09	0.011	0.760	1.50	12.3	10.8	20.8	0.760	0.290	0.040	0.002	0.002	0.011
10	0.011	0.660	1.25	6.27	17.9	11.3	0.760	0.210	0.082	0.011	0.002	0.002
11	0.011	0.460	1.50	5.35	41.4	11.8	0.760	0.210	0.140	0.011	0.001	0.001
12	0.011	0.460	1.60	3.97	15.6	11.3	0.760	0.210	0.082	0.002	KURU	0.001
13	0.011	1.90	1.50	6.50	8.50	6.04	0.660	0.210	0.140	0.002	KURU	0.001
14	0.011	9.00	1.25	5.81	6.70	4.89	0.660	0.210	0.290	0.011	KURU	0.001
15	0.011	8.75	1.10	3.28	5.58	6.50	0.560	0.140	0.290	0.011	KURU	0.001
16	0.290	1.90	1.35	2.36	4.89	3.74	0.560	0.140	0.210	0.011	KURU	0.001
17	0.082	0.980	2.59	1.90	7.10	3.05	0.560	0.140	0.210	0.011	KURU	0.001
18	0.040	1.50	3.28	1.60	32.5	2.59	0.560	0.140	0.140	0.002	KURU	0.001
19	0.040	3.28	41.4	5.58	34.0	2.59	0.560	0.140	0.140	KURU	KURU	0.001
20	0.140	15.9	13.5	10.0	31.0	1.90	0.560	0.082	0.082	KURU	KURU	0.001
21	0.082	37.5	5.12	6.27	20.4	1.90	0.560	0.082	0.082	KURU	KURU	0.001
22	0.040	7.50	3.05	4.89	13.8	1.75	0.560	0.082	0.040	0.002	KURU	0.001
23	0.040	2.13	6.04	4.43	10.3	1.60	0.460	0.082	0.040	0.002	KURU	0.001
24	0.040	8.30	6.70	4.20	7.70	1.50	0.460	0.082	0.040	0.011	KURU	0.001
25	0.040	3.74	5.35	4.20	6.27	1.50	0.460	0.082	0.040	0.002	KURU	0.011
26	0.040	4.66	8.30	6.04	9.50	1.35	0.460	0.082	0.040	0.011	KURU	0.002
27	0.040	1.75	6.90	4.89	6.04	1.25	0.380	0.040	0.040	0.011	KURU	0.001
28	0.040	1.35	5.35	4.43	4.89	1.10	0.380	0.040	0.040	0.001	KURU	0.001
29	0.040	3.28	3.74	4.20	-----	0.980	0.380	0.040	0.040	KURU	KURU	0.002
30	1.25	2.13	2.82	3.97	-----	0.980	0.380	0.040	0.040	KURU	KURU	0.040
31	6.70	-----	3.28	3.97	-----	0.980	-----	0.040	-----	KURU	KURU	-----
Maks.	41.4	91.0	71.5	27.5	42.6	39.6	0.980	0.380	0.380	0.040	0.011	0.140
Min.	0.011	0.380	1.10	1.50	4.20	0.980	0.380	0.040	0.002	KURU	KURU	KURU
Ortalama	0.294	5.97	4.80	4.33	13.2	4.93	0.623	0.171	0.082	0.007	0.000	0.003
LT/SN/Km2	2.45	49.8	40.0	36.1	110.	41.1	5.19	1.43	0.684	0.054	0.002	0.025
AKIM mm.	6.56	129.	107.	96.7	267.	110.	13.4	3.83	1.77	0.145	0.006	0.066
MİL. M3	0.787	15.5	12.8	11.6	32.0	13.2	1.61	0.459	0.213	0.017	0.001	0.008

SU YILI (2006) YILLIK TOPLAM AKIM 88.20 MİLYON M3 735 MM. 23.3 LT/SN/Km2

02. Marmara Havzasi

D02A100 KURUDERE PARGALI

YERİ : **KANDIRA AĞVA YOLU 7. KM SİNDEN BAĞIRGANLI KÖYÜ SAPAĞINDAN 5 KM SONRA KARAYOLU KÖPRÜSÜNÜN MENBAĞINDADIR. PAFTA 25.000:İST-F23-C3**
30°1'13" Doğu - 41°6'57" Kuzey

YAĞIŞ ALANI : **37,00 km2** **YAKLAŞIK KOT : 7 m**

GÖZLEM SÜRESİ : **16.05.1989 - 30.09.2006**

ORTALAMA AKIMLAR : **Gözlem süresinde 0.779 m3/sn. (17 Yıllık) 2006 Su yılında 0.915 m3/sn.**

ANLIK EN ÇOK VE EN AZ AKIMLAR:

2006 Su yılında anlık ençok akım	:	**8.99**	**m3/sn**	**05.11.2005**
2006 Su yılında anlık enaz akım	:	**0.012**	**m3/sn**	**29.07.2006**
Gözlem süresinde anlık ençok akım	:	**23.6**	**m3/sn**	**18.10.1989**
Gözlem süresinde anlık enaz akım	:	**0.000**	**m3/sn**	**01.10.1993**

2. Anahtar Eğrisi (Seviyeler cm olarak)

Seviye	Akım	Seviye	Akım	Seviye	Akım	Seviye	Akım
12	0.000	37	0.940	62	3.6	150	14.0
17	0.029	42	1.4	67	4.3	200	19.0
22	0.120	47	1.9	72	4.9		
27	0.310	52	2.4	77	5.5		
32	0.600	57	3.0	100	8.4		

Akımlar 01 Ekim 2005 'den 30 Eylül 2006' a kadar m3/sn olarak

Gün	Ekim	Kasım	Aralık	Ocak	Şubat	Mart	Nisan	Mayıs	Haziran	Temmuz	Ağustos	Eylül
01	0.029	1.40	0.800	1.30	1.60	2.20	0.740	0.310	0.096	0.072	0.019	0.019
02	0.029	0.800	0.740	1.25	1.80	1.90	0.680	0.310	0.096	0.056	0.012	0.019
03	0.029	0.600	1.15	1.05	1.90	2.20	0.680	0.310	0.096	0.041	0.012	0.019
04	0.029	1.30	1.05	0.940	2.00	1.80	0.680	0.310	0.096	0.041	0.012	0.019
05	0.029	3.35	0.940	0.860	2.00	1.60	0.600	0.310	0.096	0.041	0.012	0.019
06	0.029	1.60	0.860	0.800	4.40	1.50	0.600	0.270	0.072	0.056	0.012	0.019
07	0.029	1.05	0.800	0.940	3.60	1.60	0.600	0.310	0.072	0.041	0.012	0.019
08	0.072	0.740	0.680	1.30	3.60	2.90	0.540	0.310	0.096	0.041	0.012	0.029
09	0.041	0.600	0.600	2.10	3.35	3.80	0.540	0.310	0.096	0.041	0.012	0.029
10	0.029	0.460	0.600	2.20	4.40	3.00	0.540	0.310	0.150	0.072	0.012	0.029
11	0.029	0.360	0.540	2.20	6.47	2.90	0.540	0.310	0.120	0.072	0.012	0.029
12	0.029	0.310	0.600	3.10	4.70	2.75	0.540	0.210	0.096	0.056	0.012	0.029
13	0.029	1.15	0.600	2.90	3.95	2.40	0.540	0.270	0.150	0.072	0.012	0.029
14	0.029	3.00	0.540	3.00	3.35	2.10	0.540	0.270	0.210	0.072	0.012	0.029
15	0.041	1.90	0.460	2.30	2.90	2.10	0.540	0.270	0.180	0.072	0.012	0.029
16	0.056	1.30	0.540	2.10	2.60	1.80	0.460	0.210	0.150	0.072	0.012	0.029
17	0.056	1.05	0.540	1.80	2.60	1.70	0.460	0.210	0.120	0.072	0.012	0.029
18	0.180	0.940	1.50	1.60	5.15	1.60	0.460	0.210	0.120	0.056	0.012	0.029
19	0.120	0.940	6.59	2.30	4.70	1.50	0.400	0.210	0.120	0.041	0.012	0.041
20	0.096	3.95	4.50	2.70	5.15	1.40	0.400	0.210	0.096	0.041	0.012	0.041
21	0.096	4.90	2.90	2.30	4.50	1.30	0.400	0.180	0.096	0.041	0.012	0.041
22	0.072	2.75	2.20	2.20	3.95	1.25	0.400	0.180	0.072	0.029	0.012	0.041
23	0.056	2.20	2.40	2.10	3.50	1.15	0.310	0.180	0.072	0.029	0.012	0.041
24	0.041	2.30	2.20	1.90	3.10	1.05	0.360	0.180	0.056	0.041	0.012	0.041
25	0.041	1.90	2.00	1.90	2.90	0.940	0.360	0.180	0.056	0.029	0.012	0.041
26	0.041	1.90	2.30	1.90	2.90	0.940	0.360	0.180	0.096	0.029	0.012	0.056
27	0.041	1.50	2.20	1.70	2.40	0.860	0.360	0.150	0.072	0.019	0.012	0.041
28	0.056	1.30	2.30	1.60	2.20	0.800	0.360	0.150	0.072	0.019	0.012	0.041
29	0.072	1.25	2.20	1.50	-----	0.800	0.360	0.210	0.072	0.019	0.012	0.041
30	0.150	1.05	1.90	1.50	-----	0.740	0.360	0.150	0.072	0.012	0.012	0.056
31	1.80	-----	1.70	1.50	-----	0.740	-----	0.150	-----	0.019	0.019	-----
Maks.	2.60	8.99	8.15	7.43	8.63	5.10	0.800	0.460	0.310	0.210	0.029	0.072
Min.	0.029	0.210	0.460	0.740	1.60	0.680	0.270	0.120	0.041	0.012	0.012	0.019
Ortalama	0.112	1.59	1.58	1.83	3.42	1.72	0.490	0.236	0.102	0.046	0.012	0.032
LT/SN/Km2	3.03	43.1	42.7	49.6	92.3	46.5	13.3	6.39	2.76	1.23	0.337	0.877
AKIM mm.	8.12	112.	114.	133.	223.	125.	34.3	17.1	7.15	3.30	0.901	2.27
MİL. M3	0.300	4.13	4.23	4.91	8.27	4.61	1.27	0.633	0.265	0.122	0.033	0.084

SU YILI (2006) YILLIK TOPLAM AKIM 28.86 MİLYON M3 780 MM. 24.7 LT/SN/Km2

02. Marmara Havzasi

D02A101 YILGIN D. ÇELEBİKÖY

YERİ : **AĞVA KANDIRA YOLUNUN 5. KM SİNDE KARAYOLU KÖPRÜSÜNDEDİR PAFTA:25.000 İST-F23-C3**
29°53'58" Doğu - 41°5'32" Kuzey

YAĞIŞ ALANI : **17,50 km2** **YAKLAŞIK KOT : 27 m**

GÖZLEM SÜRESİ : **01.05.1989 - 30.09.2006**

ORTALAMA AKIMLAR : **Gözlem süresinde 0.222 m3/sn. (17 Yıllık) 2006 Su yılında 0.308 m3/sn.**

ANLIK EN ÇOK VE EN AZ AKIMLAR:

2006 Su yılında anlık ençok akım	:	**8.36**	**m3/sn**	**13.11.2005**
2006 Su yılında anlık enaz akım	:	**0.000**	**m3/sn**	**05.08.2006**
Gözlem süresinde anlık ençok akım	:	**11.9**	**m3/sn**	**08.12.1991**
Gözlem süresinde anlık enaz akım	:	**0.000**	**m3/sn**	**30.09.1993**

1. Anahtar Eğrisi (Seviyeler cm olarak)

Seviye	Akım	Seviye	Akım	Seviye	Akım	Seviye	Akım
38	0.001	53	0.500	68	1.3	160	6.5
41	0.060	56	0.640	80	2.0	170	7.1
44	0.140	59	0.780	110	3.6	180	7.7
47	0.260	62	0.920	140	5.3	250	11.9
50	0.370	65	1.1	150	5.9		

Akımlar 01 Ekim 2005 'den 30 Eylül 2006' a kadar m3/sn olarak

Gün	Ekim	Kasım	Aralık	Ocak	Şubat	Mart	Nisan	Mayıs	Haziran	Temmuz	Ağustos	Eylül
01	0.035	0.690	0.300	0.410	0.640	0.600	0.180	0.060	0.017	0.017	0.001	0.001
02	0.017	0.410	0.260	0.370	0.740	0.550	0.180	0.060	0.035	0.017	0.001	0.017
03	0.017	0.300	0.370	0.330	0.740	0.640	0.180	0.060	0.017	0.017	0.001	0.035
04	0.017	0.370	0.370	0.330	0.740	0.600	0.180	0.060	0.017	0.017	0.001	0.017
05	0.017	0.460	0.330	0.330	0.740	0.550	0.140	0.060	0.035	0.017	0.001	0.017
06	0.035	0.460	0.330	0.330	1.62	0.500	0.140	0.060	0.017	0.017	0.001	0.017
07	0.035	0.330	0.300	0.330	1.35	0.550	0.140	0.060	0.017	0.017	0.001	0.017
08	0.017	0.260	0.300	0.500	1.30	1.20	0.140	0.060	0.035	0.017	0.017	0.017
09	0.017	0.180	0.300	0.980	1.20	1.40	0.140	0.060	0.035	0.001	0.017	0.017
10	0.017	0.180	0.300	1.05	1.46	1.05	0.110	0.060	0.110	0.017	0.001	0.017
11	0.035	0.140	0.260	0.870	2.15	0.820	0.110	0.060	0.060	0.017	0.001	0.035
12	0.060	0.110	0.260	1.15	1.57	0.740	0.110	0.035	0.035	0.017	0.001	0.017
13	0.060	1.90	0.260	1.05	1.20	0.600	0.110	0.035	0.060	0.017	0.001	0.017
14	0.035	1.10	0.260	0.870	0.980	0.550	0.110	0.035	0.080	0.017	0.017	0.017
15	0.060	0.690	0.260	0.780	0.870	0.600	0.080	0.035	0.060	0.001	0.001	0.035
16	0.460	0.500	0.300	0.690	0.780	0.550	0.080	0.035	0.060	0.001	0.001	0.017
17	0.600	0.370	0.330	0.640	0.780	0.500	0.080	0.035	0.035	0.001	0.001	0.035
18	0.370	0.330	0.600	0.550	1.40	0.460	0.080	0.035	0.035	0.001	0.001	0.035
19	0.300	0.330	2.15	0.820	1.57	0.410	0.080	0.035	0.035	0.017	KURU	0.035
20	0.300	1.73	1.30	0.980	1.57	0.370	0.080	0.035	0.035	0.017	0.001	0.035
21	0.210	1.62	0.820	0.870	1.35	0.330	0.080	0.035	0.017	0.001	0.001	0.035
22	0.140	0.870	0.640	0.820	1.15	0.300	0.080	0.035	0.017	0.017	0.001	0.035
23	0.110	0.640	0.600	0.740	0.980	0.300	0.080	0.035	0.017	0.001	0.001	0.035
24	0.110	0.690	0.550	0.690	0.870	0.300	0.080	0.035	0.017	0.017	0.001	0.035
25	0.080	0.600	0.550	0.690	0.780	0.260	0.080	0.035	0.017	0.001	0.001	0.035
26	0.080	0.550	0.600	0.690	0.780	0.260	0.080	0.035	0.017	0.001	0.001	0.035
27	0.060	0.500	0.690	0.600	0.690	0.210	0.060	0.035	0.017	0.001	0.001	0.035
28	0.060	0.410	0.740	0.550	0.640	0.210	0.060	0.035	0.017	0.001	0.001	0.035
29	0.060	0.370	0.690	0.550	-----	0.210	0.060	0.035	0.035	0.001	0.001	0.035
30	0.260	0.300	0.550	0.550	-----	0.210	0.060	0.017	0.017	0.001	0.001	0.035
31	1.15	-----	0.500	0.550	-----	0.180	-----	0.035	-----	0.001	0.001	-----
Maks.	2.21	8.36	2.90	2.02	3.00	1.73	0.180	0.060	0.500	0.017	0.017	0.060
Min.	0.001	0.110	0.260	0.300	0.600	0.180	0.060	0.017	0.017	0.001	KURU	0.001
Ortalama	0.156	0.580	0.518	0.666	1.09	0.516	0.106	0.043	0.034	0.010	0.003	0.027
LT/SN/Km2	8.89	33.1	29.6	38.1	62.5	29.5	6.04	2.47	1.94	0.559	0.144	1.52
AKIM mm.	23.8	85.9	79.3	102.	151.	79.0	15.7	6.63	5.03	1.50	0.385	3.95
MİL. M3	0.417	1.50	1.39	1.79	2.65	1.38	0.274	0.116	0.088	0.026	0.007	0.069

SU YILI (2006) YILLIK TOPLAM AKIM 9.71 MİLYON M3 555 MM. 17.6 LT/SN/Km2

02. Marmara Havzasi

D02A102 KABAKÖZ D. KABAKÖZ

YERİ : **SİLE - AĞVA YOLUNUN 12. KM SİNDEKİ KABAKÖZ KÖYÜNDEDİR. PAFTA 25.000:İST-F23-D2**
29°41'22" Doğu - 41°8'32" Kuzey

YAĞIŞ ALANI : **80,50 km2** **YAKLAŞIK KOT : 5 m**

GÖZLEM SÜRESİ : **17.05.1989 - 30.09.2006**

ORTALAMA AKIMLAR : **Gözlem süresinde 1.362 m3/sn. (17 Yıllık) 2006 Su yılında 1.736 m3/sn.**

ANLIK EN ÇOK VE EN AZ AKIMLAR:

2006 Su yılında anlık ençok akım	:	**44.4**	**m3/sn**	**10.06.2006**
2006 Su yılında anlık enaz akım	:	**0.051**	**m3/sn**	**07.09.2006**
Gözlem süresinde anlık ençok akım	:	**92.3**	**m3/sn**	**13.08.1997**
Gözlem süresinde anlık enaz akım	:	**0.040**	**m3/sn**	**21.07.1998**

2. Anahtar Eğrisi (Seviyeler cm olarak)

Seviye	Akım	Seviye	Akım	Seviye	Akım	Seviye	Akım
106	0.014	270	11.0	470	44.0	670	86.8
125	0.540	310	15.0	510	52.0	680	89.0
150	1.8	350	21.0	550	60.4	690	91.2
190	4.2	390	28.0	590	69.2	700	93.4
230	7.0	430	36.0	630	78.0		

Akımlar 01 Ekim 2005 'den 30 Eylül 2006' a kadar m3/sn olarak

Gün	Ekim	Kasım	Aralık	Ocak	Şubat	Mart	Nisan	Mayıs	Haziran	Temmuz	Ağustos	Eylül
01	0.153	2.22	0.873	1.75	3.55	3.09	0.728	0.499	0.242	0.179	0.128	0.102
02	0.128	0.681	0.824	1.38	4.27	2.28	0.681	0.499	0.242	0.179	0.128	0.153
03	0.179	0.540	2.63	1.18	4.45	5.80	0.634	0.458	0.242	0.179	0.128	0.128
04	0.179	0.824	1.44	1.02	4.39	3.32	0.587	0.458	0.242	0.179	0.128	0.077
05	0.153	1.70	1.18	0.971	3.85	2.34	0.587	0.458	0.242	0.179	0.128	0.077
06	0.128	1.23	0.971	0.922	14.0	2.04	0.540	0.458	0.242	0.179	0.102	0.077
07	0.128	0.728	0.873	1.23	6.93	3.85	0.540	0.458	0.242	0.179	0.102	0.051
08	0.128	0.540	0.873	4.51	5.65	10.3	0.499	0.458	0.242	0.179	0.102	0.051
09	0.128	0.458	1.38	9.20	5.35	10.1	0.499	0.458	1.12	0.179	0.102	0.051
10	0.128	0.418	0.922	6.93	8.90	5.88	0.499	0.458	12.6	0.179	0.102	0.051
11	0.128	0.418	1.07	6.18	19.4	5.58	0.499	0.458	0.922	0.179	0.102	0.051
12	0.242	0.377	1.18	5.28	7.80	4.98	0.458	0.377	0.499	0.179	0.102	0.077
13	0.305	0.458	1.02	4.90	5.88	3.09	0.458	0.377	0.499	0.179	0.102	0.077
14	0.153	1.86	0.922	5.88	4.57	2.74	0.458	0.377	1.28	0.179	0.102	0.051
15	0.305	1.54	0.873	4.09	3.85	3.43	0.418	0.377	0.499	0.179	0.102	0.051
16	3.32	0.681	1.38	3.14	3.26	2.34	0.418	0.377	0.377	0.128	0.102	0.051
17	0.971	0.540	1.86	2.28	4.57	2.04	0.418	0.377	0.336	0.128	0.102	0.051
18	0.458	0.540	4.03	1.80	14.4	1.86	0.458	0.377	0.305	0.128	0.102	0.051
19	0.587	0.681	23.3	10.6	12.6	1.75	0.458	0.305	0.273	0.128	0.102	0.077
20	0.336	11.6	5.95	8.40	13.1	1.64	0.499	0.305	0.273	0.128	0.077	0.102
21	0.242	9.90	3.03	4.63	10.0	1.49	0.540	0.305	0.273	0.128	0.077	0.128
22	0.210	2.16	2.04	3.97	8.30	1.33	0.499	0.305	0.273	0.128	0.077	0.128
23	0.179	1.49	2.97	4.21	6.55	1.23	0.540	0.305	0.242	0.128	0.077	0.305
24	0.179	3.49	3.26	3.43	5.28	1.18	0.540	0.305	0.242	0.128	0.102	0.418
25	0.179	2.10	2.74	3.20	4.75	1.12	0.540	0.305	0.242	0.128	0.102	0.634
26	0.179	3.91	4.21	2.80	5.43	1.07	0.499	0.305	0.242	0.128	0.102	0.210
27	0.153	1.64	5.05	2.40	4.39	1.02	0.499	0.305	0.242	0.128	0.102	0.179
28	0.153	1.18	4.98	2.22	3.14	0.971	0.499	0.242	0.210	0.128	0.102	0.179
29	0.153	1.18	3.09	2.22	-----	0.873	0.499	0.242	0.210	0.128	0.102	0.179
30	1.18	0.971	1.98	2.28	-----	0.824	0.499	0.242	0.210	0.128	0.102	0.179
31	10.7	-----	2.16	2.80	-----	0.824	-----	0.242	-----	0.102	0.102	-----
Maks.	19.4	27.8	36.8	28.4	33.4	16.2	0.775	0.499	44.4	0.210	0.128	8.00
Min.	0.128	0.377	0.824	0.873	2.91	0.824	0.418	0.242	0.210	0.102	0.077	0.051
Ortalama	0.701	1.87	2.87	3.74	7.09	2.92	0.516	0.370	0.777	0.152	0.103	0.133
LT/SN/Km2	8.71	23.2	35.7	46.4	88.1	36.2	6.41	4.60	9.65	1.89	1.28	1.65
AKIM mm.	23.3	60.2	95.6	124.	213.	97.0	16.6	12.3	25.0	5.05	3.43	4.29
MİL. M3	1.88	4.84	7.69	10.0	17.2	7.81	1.34	0.991	2.01	0.407	0.276	0.345

SU YILI (2006) YILLIK TOPLAM AKIM 54.79 MİLYON M3 681 MM. 21.6 LT/SN/Km2

02. Marmara Havzasi

D02A104 KUMCAĞIZ D. KEFKEN

YERİ : KANDIRA KEFKEN YOLU ÜZERİNDEKİ KURTYERİ KÖYÜNDEN SAĞA SAPILIR. İSTASYON GİRİŞTEKİ KÖPRÜDEDİR. PAFTA 25.000:EREĞ-F24-D3
30°14'47" Doğu - 41°8'39" Kuzey

YAĞIŞ ALANI : 49,20 km2 **YAKLAŞIK KOT** : 5 m

GÖZLEM SÜRESİ : 27.05.1989 - 30.09.2006

ORTALAMA AKIMLAR : Gözlem süresinde 0.724 m3/sn. (17 Yıllık) 2006 Su yılında 1.032 m3/sn.

ANLIK EN ÇOK VE EN AZ AKIMLAR:

2006 Su yılında anlık ençok akım	:	41.1	m3/sn	20.11.2005
2006 Su yılında anlık enaz akım	:	0.001	m3/sn	11.08.2006
Gözlem süresinde anlık ençok akım	:	48.6	m3/sn	02.12.2001
Gözlem süresinde anlık enaz akım	:	0.000	m3/sn	01.10.1989

2. Anahtar Eğrisi (Seviyeler cm olarak)

Seviye	Akım	Seviye	Akım	Seviye	Akım	Seviye	Akım
75	0.000	160	4.8	250	20.0	300	33.0
80	0.007	180	7.5	260	22.0	310	36.0
100	0.220	200	10.8	270	24.0	320	39.0
120	1.0	220	14.3	280	27.0	330	42.0
140	2.5	240	18.0	290	30.0	340	45.0

Akımlar 01 Ekim 2005 'den 30 Eylül 2006' a kadar m3/sn olarak

Gün	Ekim	Kasım	Aralık	Ocak	Şubat	Mart	Nisan	Mayıs	Haziran	Temmuz	Ağustos	Eylül
01	0.006	5.45	0.560	0.654	2.34	1.16	0.322	0.189	0.013	0.007	0.007	0.030
02	0.007	0.654	0.458	0.526	3.16	0.607	0.288	0.189	0.013	0.007	0.006	0.018
03	0.058	0.654	2.72	0.458	3.38	2.42	0.254	0.173	0.024	0.007	0.006	0.007
04	0.018	4.32	0.889	0.424	3.84	0.889	0.254	0.158	0.018	0.007	0.006	0.006
05	0.006	5.45	1.70	0.390	3.27	0.654	0.254	0.158	0.007	0.007	0.004	0.007
06	0.004	2.42	0.560	0.390	17.6	0.526	0.254	0.142	0.013	0.007	0.004	0.004
07	0.004	0.795	0.390	0.390	5.19	0.842	0.220	0.142	0.013	0.007	0.004	0.004
08	0.004	0.492	0.322	0.842	9.44	6.10	0.220	0.126	0.013	0.007	0.003	0.004
09	0.004	0.322	0.526	2.26	6.80	10.3	0.322	0.111	0.013	0.007	0.003	0.006
10	0.003	0.220	0.288	2.18	14.1	2.10	0.288	0.080	0.018	0.007	0.003	0.006
11	0.004	0.189	0.424	1.50	17.1	1.37	0.254	0.064	0.018	0.007	0.001	0.006
12	0.004	0.158	0.356	2.94	4.56	1.43	0.288	0.058	0.018	0.007	0.001	0.006
13	0.006	0.158	0.254	1.57	3.72	1.03	0.254	0.111	0.024	0.007	0.001	0.006
14	0.006	5.45	0.204	1.23	2.83	1.30	0.220	0.064	0.058	0.007	0.001	0.004
15	0.006	1.86	0.204	0.748	2.26	2.10	0.220	0.058	0.041	0.007	0.001	0.004
16	0.041	0.607	0.607	0.654	2.02	1.10	0.220	0.064	0.036	0.007	0.001	0.004
17	0.936	0.390	0.795	0.560	3.60	0.889	0.220	0.080	0.030	0.007	0.003	0.004
18	0.126	0.748	1.43	0.458	11.1	0.748	0.220	0.058	0.018	0.007	0.003	0.006
19	0.041	1.57	19.8	2.34	6.10	0.842	0.220	0.058	0.018	0.007	0.003	0.006
20	0.041	13.8	2.72	5.71	3.72	0.654	0.254	0.053	0.018	0.006	0.003	0.007
21	0.095	12.0	1.37	2.26	1.86	0.607	0.254	0.047	0.013	0.006	0.003	0.036
22	0.080	1.43	0.842	1.43	1.23	0.526	0.254	0.030	0.013	0.006	0.003	0.007
23	0.024	0.889	3.38	1.30	0.936	0.492	0.254	0.030	0.013	0.006	0.001	0.006
24	0.013	5.32	3.60	1.23	0.842	0.560	0.254	0.036	0.013	0.007	0.001	0.006
25	0.013	1.70	2.10	1.37	0.842	0.560	0.220	0.041	0.013	0.006	0.003	1.23
26	0.013	2.61	3.96	3.60	2.61	0.492	0.204	0.036	0.007	0.006	0.003	0.047
27	0.013	0.936	2.34	2.72	1.23	0.424	0.204	0.036	0.007	0.006	0.004	0.013
28	0.013	0.607	1.16	2.34	0.842	0.390	0.189	0.036	0.007	0.006	0.004	0.007
29	0.018	2.61	0.889	2.18	-----	0.356	0.204	0.030	0.007	0.006	0.006	0.013
30	0.795	1.16	0.701	1.94	-----	0.356	0.204	0.024	0.007	0.006	0.004	0.024
31	3.72	-----	0.842	1.86	-----	0.356	-----	0.018	-----	0.006	0.006	-----
Maks.	13.4	41.1	35.1	18.0	36.0	17.8	0.356	0.204	0.080	0.007	0.007	9.27
Min.	0.003	0.158	0.204	0.356	0.795	0.322	0.189	0.018	0.007	0.006	0.001	0.003
Ortalama	0.197	2.50	1.82	1.56	4.88	1.36	0.243	0.081	0.017	0.007	0.003	0.051
LT/SN/Km2	4.01	50.8	37.0	31.8	99.1	27.7	4.94	1.64	0.355	0.135	0.067	1.04
AKIM mm.	10.8	132.	99.0	85.1	240.	74.1	12.8	4.39	0.920	0.362	0.179	2.69
MİL. M3	0.529	6.48	4.87	4.19	11.8	3.64	0.630	0.216	0.045	0.018	0.009	0.133

SU YILI (2006) YILLIK TOPLAM AKIM 32.56 MİLYON M3 662 MM. 21.0 LT/SN/Km2

02. Marmara Havzasi

D02A105 KOVANLİK DERESI Boztas

YERİ : CANAKKALE ILI YENICE ILCESI AKCAKOYUN BELDE`SINE 12 KM.MESAFEDE BOZTAS MEVKII`NDEKI ESKI KOPRU BACAGINDADIR.
27°6'18" Doğu - 39°46'11" Kuzey

YAĞIŞ ALANI : 73.50 km2 YAKLAŞIK KOT : 320 m

GÖZLEM SÜRESİ : 21.09.1989 - 30.09.2006

ORTALAMA AKIMLAR : Gözlem süresinde 2.604 m3/sn. (14 Yıllık) 2006 Su yılında 4.952 m3/sn.

ANLIK EN ÇOK VE EN AZ AKIMLAR:

2006 Su yılında anlık ençok akım	:	80.5	m3/sn	25.11.2005
2006 Su yılında anlık enaz akım	:	0.180	m3/sn	24.08.2006
Gözlem süresinde anlık ençok akım	:	198.	m3/sn	25.12.1995
Gözlem süresinde anlık enaz akım	:	0.080	m3/sn	28.08.2000

7. Anahtar Eğrisi (Seviyeler cm olarak)

Seviye	Akım	Seviye	Akım	Seviye	Akım	Seviye	Akım
14	0.000	36	1.6	100	23.0	230	84.0
17	0.150	46	3.5	130	35.5	250	95.0
19	0.235	60	7.3	150	44.6	400	185.
24	0.500	80	15.0	170	54.0	420	197.
30	0.990	87	17.8	210	74.0	440	209.

Akımlar 01 Ekim 2005 'den 30 Eylül 2006' a kadar m3/sn olarak

Gün	Ekim	Kasım	Aralık	Ocak	Şubat	Mart	Nisan	Mayıs	Haziran	Temmuz	Ağustos	Eylül
01	0.270	0.380	6.80	26.6	8.63	19.0	4.81	1.82	0.807	0.453	0.253	0.217
02	0.800	0.380	6.20	21.8	8.63	16.2	4.52	1.82	0.723	0.515	0.253	0.217
03	0.500	0.380	5.60	19.4	8.00	23.0	4.32	1.82	0.723	0.515	0.253	0.217
04	0.380	0.325	5.08	18.2	7.40	18.6	4.32	1.82	0.723	0.515	0.253	0.217
05	0.325	0.325	4.65	16.6	9.29	15.4	3.91	1.82	0.723	0.515	0.253	0.217
06	0.325	0.270	4.43	15.8	11.3	13.0	3.91	1.82	0.723	0.453	0.253	0.217
07	0.325	0.270	4.22	14.3	10.6	21.4	3.71	1.82	0.723	0.453	0.253	0.217
08	0.270	0.270	3.23	13.3	9.95	27.0	3.91	1.82	0.723	0.390	0.253	0.217
09	0.270	0.270	3.04	12.6	9.62	20.6	3.71	1.68	0.723	0.340	0.253	0.217
10	0.270	0.270	3.04	11.9	15.0	16.2	3.71	1.55	0.723	0.340	0.253	0.217
11	0.325	0.270	2.85	11.6	19.8	17.4	3.31	1.68	0.723	0.340	0.253	0.253
12	0.435	0.270	2.67	10.9	15.8	22.2	3.31	1.68	0.723	0.340	0.253	0.253
13	0.380	0.270	2.67	10.6	13.6	19.8	3.11	1.55	0.723	0.340	0.253	0.253
14	0.380	0.270	2.49	10.3	12.6	19.8	3.11	1.55	0.807	0.340	0.253	0.253
15	0.325	0.270	2.49	9.62	11.6	17.4	2.90	1.55	0.807	0.340	0.217	0.217
16	0.325	0.270	2.85	9.29	8.30	15.4	2.90	1.28	0.807	0.340	0.217	0.217
17	0.270	0.500	2.85	8.96	5.60	13.0	2.70	1.14	0.723	0.390	0.217	0.217
18	0.270	1.12	7.70	8.96	8.63	11.4	2.50	1.14	0.640	0.390	0.217	0.217
19	0.270	0.800	10.9	19.8	11.6	10.3	2.50	1.14	0.578	0.340	0.217	0.217
20	0.270	1.20	8.30	18.6	16.2	9.20	2.50	1.14	0.578	0.340	0.217	0.217
21	0.270	0.570	6.80	15.0	14.7	7.76	2.36	1.14	0.578	0.290	0.217	0.217
22	0.270	0.380	5.90	14.0	13.0	7.11	2.36	1.06	0.515	0.290	0.217	0.290
23	0.270	0.570	5.30	13.3	11.6	6.54	2.36	1.06	0.515	0.290	0.217	0.253
24	0.270	16.2	4.87	12.3	11.3	7.76	2.36	1.06	0.515	0.290	0.217	0.578
25	0.270	46.5	4.43	11.6	29.0	7.11	2.23	1.06	0.515	0.290	0.180	0.578
26	0.270	21.0	4.00	10.9	35.1	6.54	2.23	1.06	0.515	0.290	0.180	0.390
27	0.270	17.4	7.40	10.3	27.4	6.25	2.23	0.973	0.515	0.290	0.180	0.340
28	0.270	13.0	22.2	9.62	21.8	5.96	1.96	0.973	0.515	0.290	0.180	0.340
29	0.270	9.62	41.4	9.62	-----	5.67	1.96	0.973	0.515	0.290	0.180	3.11
30	0.380	7.40	28.6	9.29	-----	5.67	1.82	0.890	0.515	0.253	0.180	1.14
31	0.380	-----	31.5	8.96	-----	5.38	-----	0.807	-----	0.253	0.180	-----
Maks.	1.55	80.5	50.7	30.6	42.8	34.6	4.81	1.82	0.973	0.515	0.253	18.6
Min.	0.270	0.270	2.49	8.96	5.60	4.81	1.68	0.723	0.390	0.253	0.180	0.217
Ortalama	0.328	4.70	8.21	13.4	13.8	13.5	3.05	1.38	0.655	0.358	0.225	0.391
LT/SN/Km2	4.47	64.0	112.	182.	188.	183.	41.5	18.7	8.91	4.87	3.06	5.32
AKIM mm.	12.0	166.	299.	487.	454.	491.	108.	50.2	23.1	13.1	8.20	13.8
MİL. M3	0.879	12.2	22.0	35.8	33.4	36.1	7.91	3.69	1.70	0.959	0.602	1.01

SU YILI (2006) YILLIK TOPLAM AKIM 156.25 MİLYON M3 2126 MM. 67.4 LT/SN/Km2

02. Marmara Havzasi

D02A107 KILINCI D. KEMERBURGAZ

YERİ : İSTANBUL KEMERBURGAZDAN ORMAN FİDANLIĞI İÇİNDE BULUNMAKTADIR. PAFTA:İST-F21-C2
28°52'51" Doğu - 41°10'32" Kuzey

YAĞIŞ ALANI : 55,00 km2 **YAKLAŞIK KOT** : 38 m

GÖZLEM SÜRESİ : 17.05.1989 - 30.09.2006

ORTALAMA AKIMLAR : Gözlem süresinde 0.454 m3/sn. (16 Yıllık) 2006 Su yılında 0.562 m3/sn.

ANLIK EN ÇOK VE EN AZ AKIMLAR:

2006 Su yılında anlık ençok akım	:	12.5	m3/sn	19.12.2005
2006 Su yılında anlık enaz akım	:	0.052	m3/sn	21.07.2006
Gözlem süresinde anlık ençok akım	:	12.5	m3/sn	19.12.2005
Gözlem süresinde anlık enaz akım	:	0.000	m3/sn	17.08.1991

1. Anahtar Eğrisi (Seviyeler cm olarak)

Seviye	Akım	Seviye	Akım	Seviye	Akım	Seviye	Akım
25	0.000	45	0.200	65	0.930	85	1.8
29	0.000	49	0.320	69	1.1	89	1.9
33	0.000	53	0.450	73	1.2	120	3.0
37	0.008	57	0.600	77	1.4	300	9.9
41	0.080	61	0.760	81	1.6		

Akımlar 01 Ekim 2005 'den 30 Eylül 2006' a kadar m3/sn olarak

Gün	Ekim	Kasım	Aralık	Ocak	Şubat	Mart	Nisan	Mayıs	Haziran	Temmuz	Ağustos	Eylül
01	0.069	0.230	0.177	0.600	1.20	1.25	0.530	0.320	0.380	0.350	0.100	0.170
02	0.069	0.154	0.177	0.490	1.30	1.05	0.410	0.320	0.350	0.290	0.170	0.220
03	0.084	0.230	1.84	0.450	1.25	1.50	0.350	0.350	0.320	0.220	0.170	0.170
04	0.130	0.350	0.732	0.450	1.17	1.17	0.290	0.350	0.320	0.260	0.170	0.140
05	0.084	0.200	0.382	0.410	1.10	0.960	0.290	0.380	0.290	0.320	0.170	0.140
06	0.069	0.154	0.260	0.450	3.39	0.850	0.260	0.410	0.290	0.260	0.140	0.170
07	0.054	0.154	0.200	1.17	1.82	1.52	0.220	0.410	0.290	0.220	0.140	0.200
08	0.069	0.154	0.177	1.25	1.45	5.16	0.320	0.410	0.350	0.220	0.100	0.200
09	0.054	0.130	0.230	1.20	1.30	2.41	0.380	0.450	0.410	0.220	0.100	0.200
10	0.320	0.130	0.177	1.55	3.21	1.30	0.320	0.410	0.260	0.200	0.140	0.200
11	0.084	0.130	0.154	1.80	5.28	1.10	0.350	0.410	0.290	0.170	0.140	0.260
12	0.069	0.130	0.130	1.65	2.41	1.15	0.350	0.380	0.320	0.220	0.140	0.220
13	0.069	0.230	0.107	1.30	1.90	0.930	0.320	0.380	0.320	0.220	0.140	0.200
14	0.069	0.350	0.084	0.960	1.60	1.65	0.320	0.380	0.350	0.200	0.140	0.200
15	0.084	0.260	0.084	0.850	1.35	2.34	0.350	0.380	0.260	0.170	0.100	0.200
16	0.107	0.177	0.230	0.760	1.15	1.17	0.350	0.380	0.220	0.170	0.140	0.170
17	0.130	0.154	0.446	0.720	1.45	0.890	0.320	0.410	0.220	0.140	0.140	0.140
18	0.107	0.414	6.76	0.680	2.16	0.720	0.320	0.410	0.220	0.140	0.170	0.100
19	0.107	0.510	8.12	0.850	1.70	0.600	0.320	0.490	0.200	0.140	0.140	0.100
20	0.154	1.12	1.75	1.25	1.25	0.530	0.320	0.600	0.200	0.170	0.140	0.080
21	0.107	0.806	0.960	0.960	1.05	0.450	0.320	0.490	0.290	0.100	0.140	0.080
22	0.084	0.382	0.720	0.890	0.890	0.410	0.350	0.380	0.320	0.080	0.100	0.080
23	0.107	0.290	0.680	0.850	0.790	0.380	0.350	0.560	0.320	0.100	0.080	0.930
24	0.107	0.769	0.790	0.850	0.760	0.640	0.320	0.530	0.350	0.140	0.100	0.600
25	0.107	1.44	0.850	0.850	1.65	0.760	0.490	0.530	0.350	0.170	0.100	0.490
26	0.107	1.68	0.720	0.850	1.65	0.560	0.640	0.490	0.290	0.220	0.100	0.170
27	0.084	0.547	0.640	0.790	2.37	0.450	0.490	0.410	0.260	0.200	0.100	0.100
28	0.084	0.320	0.600	0.790	1.52	0.380	0.380	0.450	0.320	0.170	0.140	0.100
29	0.084	0.290	0.490	0.790	-----	0.320	0.350	0.380	0.350	0.170	0.220	0.220
30	0.290	0.177	0.450	0.850	-----	0.600	0.320	0.380	0.350	0.170	0.170	0.200
31	0.547	-----	0.640	0.930	-----	0.760	-----	0.380	-----	0.170	0.170	-----
Maks.	1.08	3.12	12.5	2.20	7.44	6.36	0.760	0.720	1.25	0.380	0.410	1.80
Min.	0.054	0.130	0.084	0.380	0.760	0.320	0.220	0.320	0.200	0.052	0.080	0.080
Ortalama	0.119	0.402	0.960	0.911	1.72	1.10	0.357	0.420	0.302	0.193	0.136	0.215
LT/SN/Km2	2.16	7.31	17.5	16.6	31.2	19.9	6.48	7.63	5.49	3.51	2.47	3.91
AKIM mm.	5.80	18.9	46.7	44.4	75.6	53.3	16.8	20.4	14.2	9.41	6.61	10.1
MİL. M3	0.319	1.04	2.57	2.44	4.16	2.93	0.924	1.12	0.783	0.518	0.364	0.557

SU YILI (2006) YILLIK TOPLAM AKIM 17.73 MİLYON M3 322 MM. 10.2 LT/SN/Km2

02. Marmara Havzasi

D02A116 SARISU D. İZZETTİN

YERİ : **ÇATALCA İLÇESİNDEN İZZETTİN MEVKİİNE GİDİLİR. İZZETTİN DEN 2 KM SONRAKİ KARAYOLU KÖPRÜSÜNÜN 5 M. MANSABINDADIR. PAFTA: 25.000 İST-F21-D1 28°31'24" Doğu - 41°11'6" Kuzey**

YAĞIŞ ALANI : **83,90 km2** **YAKLAŞIK KOT : 8 m**

GÖZLEM SÜRESİ : **17.02.1994 - 30.09.2006**

ORTALAMA AKIMLAR : **Gözlem süresinde 1.019 m3/sn. (12 Yıllık) 2006 Su yılında 1.450 m3/sn.**

ANLIK EN ÇOK VE EN AZ AKIMLAR:

2006 Su yılında anlık ençok akım	:	**124.**	**m3/sn**	**18.12.2005**
2006 Su yılında anlık enaz akım	:	**0.000**	**m3/sn**	**02.08.2006**
Gözlem süresinde anlık ençok akım	:	**159.**	**m3/sn**	**25.12.2001**
Gözlem süresinde anlık enaz akım	:	**0.000**	**m3/sn**	**28.05.1996**

6. Anahtar Eğrisi (Seviyeler cm olarak)

Seviye	Akım	Seviye	Akım	Seviye	Akım	Seviye	Akım
22	0.000	37	0.105	150	38.5	260	190.
25	0.003	40	0.180	180	63.5	270	218.
28	0.010	60	1.9	210	97.0	280	250.
31	0.026	90	8.2	240	144.	290	290.
34	0.059	120	20.3	250	166.	300	340.

Akımlar 01 Ekim 2005 'den 30 Eylül 2006' a kadar m3/sn olarak

Gün	Ekim	Kasım	Aralık	Ocak	Şubat	Mart	Nisan	Mayıs	Haziran	Temmuz	Ağustos	Eylül
01	0.008	0.034	0.264	2.03	3.10	2.94	1.08	0.264	0.059	0.014	0.001	KURU
02	0.010	0.026	0.264	1.65	4.03	2.03	0.968	0.264	0.070	0.020	KURU	KURU
03	0.014	0.026	2.18	1.42	3.40	4.45	0.854	0.264	0.070	0.090	0.001	KURU
04	0.010	0.043	0.854	1.31	2.94	2.03	0.854	0.264	0.070	0.020	0.001	KURU
05	0.010	0.026	0.530	1.20	3.61	1.77	0.740	0.222	0.059	0.014	KURU	KURU
06	0.008	0.020	0.390	1.42	12.7	1.54	0.740	0.222	0.059	0.010	KURU	KURU
07	0.010	0.026	0.348	2.03	3.25	6.04	0.670	0.222	0.059	0.010	KURU	KURU
08	0.014	0.020	0.348	2.03	4.87	22.0	0.854	0.222	0.070	0.010	KURU	KURU
09	0.010	0.020	0.670	4.24	4.03	7.66	0.740	0.222	0.070	0.010	0.003	KURU
10	0.010	0.020	0.348	11.2	14.8	4.03	0.670	0.180	0.090	0.010	0.002	KURU
11	0.014	0.020	0.306	11.9	23.7	3.25	0.600	0.180	0.059	0.010	0.005	KURU
12	0.014	0.020	0.348	14.4	7.93	2.94	0.600	0.180	0.059	0.010	0.002	KURU
13	0.008	0.020	0.306	12.7	5.29	2.34	0.460	0.180	0.070	0.010	KURU	KURU
14	0.008	0.070	0.348	7.12	3.61	6.31	0.460	0.150	0.125	0.008	KURU	KURU
15	0.008	0.059	0.306	4.24	2.79	4.87	0.460	0.125	0.059	0.008	KURU	KURU
16	0.010	0.034	0.460	2.94	2.34	4.03	0.390	0.125	0.059	0.008	KURU	KURU
17	0.020	0.034	0.854	2.49	5.77	2.94	0.390	0.125	0.043	0.008	KURU	KURU
18	0.014	0.043	36.6	2.18	11.2	2.18	0.390	0.125	0.043	0.008	KURU	KURU
19	0.014	0.125	29.0	5.08	5.29	1.88	0.390	0.125	0.034	0.008	KURU	KURU
20	0.014	0.264	4.03	4.87	4.24	1.65	0.390	0.105	0.034	0.008	KURU	KURU
21	0.014	0.670	2.34	2.64	2.94	1.42	0.348	0.105	0.034	0.005	KURU	KURU
22	0.014	0.180	2.03	2.18	2.34	1.31	0.348	0.090	0.034	0.005	KURU	KURU
23	0.010	0.125	1.77	2.03	2.03	1.20	0.348	0.105	0.034	0.005	KURU	0.125
24	0.014	1.20	1.65	2.18	1.88	3.61	0.306	0.090	0.026	0.005	KURU	0.070
25	0.014	2.18	1.54	2.79	6.04	1.88	0.306	0.090	0.020	0.005	KURU	0.348
26	0.020	2.49	1.77	2.34	5.29	1.42	0.264	0.090	0.026	0.003	KURU	0.105
27	0.014	0.670	2.64	4.45	10.8	1.31	0.306	0.090	0.020	0.002	KURU	0.034
28	0.020	0.460	2.49	3.61	3.40	1.20	0.264	0.090	0.014	0.002	KURU	0.043
29	0.014	0.348	1.77	2.03	-----	1.08	0.306	0.070	0.026	0.001	KURU	0.034
30	0.043	0.264	1.54	1.77	-----	2.49	0.306	0.070	0.020	0.001	KURU	0.043
31	0.125	-----	4.24	2.03	-----	1.54	-----	0.059	-----	0.001	KURU	-----
Maks.	0.222	10.5	124.	31.4	46.0	43.8	1.20	0.306	0.348	0.390	0.014	0.600
Min.	0.008	0.020	0.264	1.20	1.88	1.08	0.264	0.059	0.014	0.001	KURU	KURU
Ortalama	0.017	0.318	3.31	4.02	5.84	3.40	0.527	0.152	0.051	0.011	0.000	0.027
LT/SN/Km2	0.204	3.79	39.4	47.9	69.6	40.5	6.28	1.81	0.602	0.126	0.006	0.319
AKIM mm.	0.546	9.82	106.	128.	168.	108.	16.3	4.86	1.56	0.339	0.015	0.826
MİL. M3	0.046	0.824	8.86	10.8	14.1	9.10	1.37	0.407	0.131	0.028	0.001	0.069

SU YILI (2006) YILLIK TOPLAM AKIM 45.74 MİLYON M3 545 MM. 17.3 LT/SN/Km2

02. Marmara Havzasi

D02A117 ÇAKIL D. AHMEDİYE

YERİ : ÇATALCA İLÇESİNDEN B.ÇEKMECE İSTİKAMETİNE GİDERKEN AHMEDİYE MEVKİİNDEN SAĞA DOĞRU SAPILARAK 500 M. İLERDEKİ KÖPRÜ MANSABINDADIR. PAFTA :25.000 İST-F21-D4 28°29'56" Doğu - 41°6'10" Kuzey

YAĞIŞ ALANI : 55,70 km2 **YAKLAŞIK KOT :** 30 m

GÖZLEM SÜRESİ : 09.05.1994 - 30.09.2006

ORTALAMA AKIMLAR : Gözlem süresinde 0.357 m3/sn. (11 Yıllık) 2006 Su yılında 0.584 m3/sn.

ANLIK EN ÇOK VE EN AZ AKIMLAR:

2006 Su yılında anlık ençok akım	:	36.7	m3/sn	18.12.2005
2006 Su yılında anlık enaz akım	:	0.000	m3/sn	03.08.2006
Gözlem süresinde anlık ençok akım	:	44.1	m3/sn	25.12.2001
Gözlem süresinde anlık enaz akım	:	0.000	m3/sn	01.10.1994

İstasyon için kullanılmış anahtar bulunamadı.

Akımlar 01 Ekim 2005 'den 30 Eylül 2006' a kadar m3/sn olarak

Gün	Ekim	Kasım	Aralık	Ocak	Şubat	Mart	Nisan	Mayıs	Haziran	Temmuz	Ağustos	Eylül
01	0.030	0.104	0.162	1.00	1.25	1.31	0.523	0.220	0.075	0.030	0.030	0.007
02	0.050	0.075	0.191	0.682	2.07	0.947	0.470	0.220	0.075	0.030	0.001	0.050
03	0.050	0.075	1.80	0.523	1.56	2.71	0.420	0.220	0.075	0.050	KURU	0.030
04	0.030	0.104	0.420	0.420	1.25	1.00	0.370	0.270	0.050	0.030	KURU	0.050
05	0.030	0.075	0.220	0.320	1.31	0.841	0.370	0.220	0.050	0.050	KURU	0.075
06	0.030	0.075	0.191	0.370	3.17	0.788	0.370	0.220	0.050	0.075	0.001	0.050
07	0.007	0.075	0.191	0.220	1.43	3.64	0.370	0.220	0.075	0.050	0.007	0.030
08	0.007	0.104	0.220	0.191	1.37	6.22	0.420	0.220	0.104	0.007	0.050	0.007
09	0.030	0.104	0.220	0.220	1.12	3.45	0.370	0.220	0.133	0.007	0.050	0.001
10	0.030	0.104	0.191	1.19	10.8	1.98	0.370	0.191	0.133	0.030	0.007	0.001
11	0.050	0.104	0.162	4.51	9.90	1.62	0.320	0.162	0.075	0.050	0.030	0.007
12	0.050	0.075	0.162	6.46	3.17	1.56	0.320	0.191	0.075	0.050	0.007	0.001
13	0.050	0.133	0.191	2.80	2.07	1.43	0.320	0.162	0.075	0.030	0.007	0.001
14	0.050	0.162	0.220	1.62	1.37	2.89	0.320	0.162	0.075	0.030	0.030	0.001
15	0.075	0.075	0.191	0.894	1.00	2.07	0.320	0.162	0.075	0.007	0.007	0.001
16	0.104	0.075	0.220	0.629	0.894	2.25	0.270	0.162	0.104	0.050	0.007	0.001
17	0.104	0.075	0.270	0.523	1.89	1.43	0.270	0.133	0.075	0.030	0.001	0.001
18	0.104	0.191	11.3	0.420	3.74	1.00	0.270	0.133	0.075	0.075	0.001	0.007
19	0.133	0.162	7.15	1.06	1.98	0.841	0.270	0.133	0.050	0.133	0.001	0.050
20	0.133	0.220	1.56	1.00	1.89	0.735	0.270	0.133	0.050	0.104	0.001	0.030
21	0.104	0.162	0.841	0.523	1.31	0.629	0.270	0.133	0.050	0.075	0.001	0.075
22	0.075	0.104	0.682	0.420	1.12	0.576	0.220	0.162	0.050	0.050	KURU	0.075
23	0.075	0.133	0.523	0.370	0.947	0.576	0.220	0.191	0.050	0.050	KURU	0.220
24	0.075	0.320	0.470	0.320	1.06	2.71	0.220	0.162	0.030	0.075	KURU	0.162
25	0.104	1.06	0.370	0.320	3.36	1.12	0.220	0.133	0.030	0.104	KURU	0.104
26	0.162	0.841	0.523	0.470	2.99	0.788	0.270	0.104	0.050	0.075	KURU	0.050
27	0.133	0.270	0.841	0.523	5.39	0.682	0.370	0.133	0.050	0.050	KURU	0.050
28	0.133	0.191	0.682	0.470	1.71	0.576	0.270	0.104	0.050	0.075	0.001	0.104
29	0.133	0.191	0.523	0.420	-----	0.576	0.220	0.104	0.075	0.050	0.030	0.075
30	0.104	0.162	0.470	0.470	-----	1.62	0.220	0.075	0.050	0.030	0.001	0.050
31	0.162	-----	3.64	0.735	-----	0.841	-----	0.075	-----	0.030	KURU	-----
Maks.	0.220	2.52	36.7	8.54	22.7	12.7	0.576	0.420	0.162	0.470	0.191	0.894
Min.	0.007	0.050	0.162	0.191	0.788	0.576	0.191	0.075	0.007	0.007	KURU	0.001
Ortalama	0.078	0.187	1.12	0.971	2.54	1.59	0.317	0.165	0.068	0.051	0.009	0.046
LT/SN/Km2	1.39	3.35	20.2	17.4	45.6	28.6	5.69	2.97	1.22	0.916	0.157	0.817
AKIM mm.	3.73	8.69	54.0	46.7	110.	76.6	14.7	7.96	3.16	2.45	0.420	2.12
MİL. M3	0.208	0.484	3.01	2.60	6.14	4.27	0.821	0.443	0.176	0.137	0.023	0.118

SU YILI (2006) YILLIK TOPLAM AKIM 18.43 MİLYON M3 331 MM. 10.5 LT/SN/Km2

02. Marmara Havzasi

D02A119 VELİKA D. ARMUTVEREN

YERİ : **ARMUTVEREN-KARANLIKKOY YOLU 900MDEKI KOPRUDE MANSAPTADIR.E19A1**
27°33'29" Doğu - 41°53'58" Kuzey

YAĞIŞ ALANI : **342,00 km2** **YAKLAŞIK KOT : 271 m**

GÖZLEM SÜRESİ : **22.08.1995 - 30.09.2006**

ORTALAMA AKIMLAR : **Gözlem süresinde 5.702 m3/sn. (11 Yıllık) 2006 Su yılında 11.599 m3/sn.**

ANLIK EN ÇOK VE EN AZ AKIMLAR:

2006 Su yılında anlık ençok akım	**:**	**740.**	**m3/sn**	**02.07.2006**
2006 Su yılında anlık enaz akım	**:**	**1.59**	**m3/sn**	**11.10.2005**
Gözlem süresinde anlık ençok akım	**:**	**740.**	**m3/sn**	**02.07.2006**
Gözlem süresinde anlık enaz akım	**:**	**0.378**	**m3/sn**	**19.10.2001**

5. Anahtar Eğrisi (Seviyeler cm olarak)

Seviye	Akım	Seviye	Akım	Seviye	Akım	Seviye	Akım
1	0.000	16	0.450	51	9.8	221	170.
4	0.000	19	0.800	81	28.0	281	248.
7	0.000	22	1.4	111	54.0	321	300.
10	0.000	25	1.9	141	84.0	351	349.
13	0.190	36	4.3	171	114.	401	460.

Akımlar 01 Ekim 2005 'den 30 Eylül 2006' a kadar m3/sn olarak

Gün	Ekim	Kasım	Aralık	Ocak	Şubat	Mart	Nisan	Mayıs	Haziran	Temmuz	Ağustos	Eylül
01	1.82	1.59	3.42	21.8	5.57	33.0	12.5	5.57	4.28	6.80	12.0	3.42
02	1.82	1.59	3.42	16.3	6.00	18.5	12.5	6.00	4.28	149.	12.0	3.42
03	2.28	1.59	3.42	13.6	6.00	22.4	12.0	10.3	4.28	320.	12.0	2.99
04	1.82	1.59	3.19	12.5	6.00	16.9	12.0	10.3	4.28	40.4	12.0	2.56
05	1.82	1.59	3.19	11.4	6.80	14.2	12.0	10.3	4.28	25.0	12.0	2.56
06	1.82	1.59	3.19	49.6	6.00	12.5	12.0	10.3	4.28	21.3	12.0	2.56
07	1.82	1.59	2.96	37.9	5.57	21.8	12.0	10.3	4.28	20.2	11.4	2.56
08	1.82	1.59	2.96	18.5	5.57	19.6	12.5	10.3	4.28	19.6	11.4	2.56
09	1.82	1.59	3.88	14.7	5.57	16.3	12.0	8.40	39.6	19.1	11.4	2.56
10	1.82	1.59	3.42	12.5	6.00	15.2	11.4	5.57	9.20	18.5	11.4	2.56
11	1.82	1.59	3.88	10.8	6.80	47.9	11.4	5.57	7.60	18.5	11.4	2.56
12	1.82	1.59	5.54	10.5	6.80	106.	10.8	5.14	7.60	15.8	11.4	2.56
13	1.82	1.59	4.87	10.0	6.00	50.4	10.8	5.14	10.3	15.2	11.4	2.56
14	1.82	1.59	4.21	8.40	6.00	29.1	10.8	5.14	10.8	14.7	10.3	2.56
15	1.82	1.59	4.21	7.60	5.57	21.8	10.8	5.14	10.3	14.2	4.28	2.56
16	1.82	1.59	4.54	6.80	5.57	19.6	10.8	5.14	10.0	13.6	3.85	2.56
17	1.82	2.74	4.87	6.80	10.5	18.5	10.8	5.14	10.0	13.6	3.85	2.56
18	1.59	3.88	4.87	6.00	29.1	18.5	10.8	5.14	9.20	13.6	3.85	2.56
19	1.59	4.87	4.54	16.9	31.4	17.4	10.8	5.14	8.40	13.6	3.85	2.56
20	1.59	6.20	4.21	13.1	33.0	16.9	10.8	5.14	8.40	13.6	3.85	2.99
21	1.59	3.42	4.21	10.5	23.6	16.3	10.8	5.14	8.40	13.6	3.85	2.99
22	1.59	2.74	4.21	10.3	20.2	16.3	10.5	4.71	8.40	13.6	3.85	3.42
23	1.59	2.51	4.21	10.0	16.9	16.9	10.5	4.71	8.40	13.6	3.85	4.71
24	1.59	12.0	3.88	9.20	15.2	16.9	10.5	4.71	6.80	13.1	3.85	4.28
25	1.59	46.2	3.88	9.20	15.2	15.8	10.5	4.71	6.80	13.1	3.42	2.99
26	1.59	12.0	3.88	9.20	22.9	15.2	10.5	4.71	7.60	13.1	2.99	2.56
27	1.59	6.20	79.1	9.20	26.4	14.7	10.5	4.71	7.60	13.1	2.99	2.56
28	1.59	5.20	246.	9.20	19.1	14.2	10.5	4.71	7.60	13.1	2.99	2.99
29	1.59	4.21	45.4	8.40	-----	14.2	10.3	4.71	7.60	12.5	2.99	6.00
30	1.59	3.65	26.4	7.60	-----	13.6	6.00	4.28	7.60	12.0	3.42	5.57
31	1.59	-----	53.8	6.00	-----	13.1	-----	4.28	-----	12.0	3.42	-----
Maks.	2.51	91.0	587.	125.	42.1	206.	14.2	10.3	228.	740.	12.0	14.7
Min.	1.59	1.59	2.96	5.57	4.28	12.5	5.57	4.28	4.28	6.80	2.99	2.56
Ortalama	1.73	4.71	17.9	13.0	12.8	22.7	11.0	6.15	8.41	30.0	7.20	3.06
LT/SN/Km2	5.06	13.8	52.2	38.2	37.5	66.4	32.2	18.0	24.6	87.6	21.1	8.95
AKIM mm.	13.6	35.7	140.	102.	90.8	178.	83.4	48.1	63.8	235.	56.4	23.2
MİL. M3	4.64	12.2	47.8	34.9	31.0	60.8	28.5	16.5	21.8	80.3	19.3	7.94

SU YILI (2006) YILLIK TOPLAM AKIM 365.68 MİLYON M3 1069 MM. 33.9 LT/SN/Km2

02. Marmara Havzasi

D02A120 KOCADERE ÇAGLAYIK

YERİ : **CAGLAYIK-KARAABALAR YOLUNUN 2. KMSİNDEKI KOPRUDE MANSAPTADIR.D18C4**
27°19'45" Doğu - 42°2'45" Kuzey

YAĞIŞ ALANI : **208,20 km2** **YAKLAŞIK KOT : 313 m**

GÖZLEM SÜRESİ : **22.08.1995 – 30.09.2006**

ORTALAMA AKIMLAR : **Gözlem süresinde 2.329 m3/sn. (11 Yıllık) 2006 Su yılında 2.043 m3/sn.**

ANLIK EN ÇOK VE EN AZ AKIMLAR:

2006 Su yılında anlık ençok akım	**:**	**83.3**	**m3/sn**	**09.06.2006**
2006 Su yılında anlık enaz akım	**:**	**0.251**	**m3/sn**	**01.10.2005**
Gözlem süresinde anlık ençok akım	**:**	**198.**	**m3/sn**	**05.12.1998**
Gözlem süresinde anlık enaz akım	**:**	**0.039**	**m3/sn**	**30.12.2002**

İstasyon için kullanılmış anahtar bulunamadı.

Akımlar 01 Ekim 2005 'den 30 Eylül 2006' a kadar m3/sn olarak

Gün	Ekim	Kasım	Aralık	Ocak	Şubat	Mart	Nisan	Mayıs	Haziran	Temmuz	Ağustos	Eylül
01	0.251	0.251	0.539	5.09	1.58	4.32	1.30	1.30	1.11	0.910	1.30	0.676
02	0.295	0.251	0.608	3.55	1.58	4.06	1.30	1.30	1.11	28.0	1.30	0.676
03	0.339	0.295	0.608	4.06	1.58	1.71	1.30	1.30	1.11	56.8	1.30	0.676
04	0.295	0.295	0.608	4.58	1.44	1.20	1.30	1.30	1.11	5.60	1.30	0.608
05	0.251	0.251	0.608	3.55	1.44	1.20	1.30	1.30	1.11	3.30	1.30	0.608
06	0.251	0.251	0.539	25.3	1.44	1.20	1.30	1.30	1.11	2.62	1.30	0.608
07	0.251	0.251	0.539	16.9	1.30	1.20	1.30	1.30	1.11	2.41	1.30	0.608
08	0.251	0.251	1.20	8.19	1.30	1.20	1.30	1.30	1.11	2.41	1.30	0.608
09	0.251	0.251	1.71	7.08	1.30	1.20	1.30	1.30	11.6	2.20	1.30	0.608
10	0.251	0.251	1.11	6.71	1.30	1.20	1.30	1.20	4.83	2.20	1.30	0.608
11	0.251	0.251	1.44	5.34	1.30	1.20	1.30	1.20	1.44	2.20	1.30	0.608
12	0.295	0.251	1.30	1.99	1.30	36.6	1.30	1.20	1.20	1.85	1.30	0.608
13	0.295	0.295	0.910	1.44	1.20	7.82	1.30	1.20	1.11	1.71	1.30	0.608
14	0.251	0.295	0.910	1.44	1.20	3.81	1.30	1.20	1.11	0.676	1.20	0.608
15	0.295	0.295	0.910	1.44	1.20	1.30	1.30	1.20	1.11	1.58	0.745	0.608
16	0.295	0.295	0.910	1.44	1.20	1.30	1.30	1.11	1.11	1.58	0.745	0.608
17	0.295	0.339	0.910	1.44	1.20	1.30	1.44	1.11	1.01	1.58	0.745	0.608
18	0.251	0.427	0.910	1.44	3.55	1.30	1.44	1.11	1.01	1.58	0.745	0.608
19	0.251	0.471	0.910	1.44	3.55	1.30	1.44	1.11	1.01	1.58	0.745	0.608
20	0.251	0.745	0.910	1.58	2.62	1.30	1.44	1.11	1.01	1.58	0.745	0.676
21	0.251	0.471	0.910	1.58	1.58	1.30	1.44	1.11	1.01	1.58	0.745	0.813
22	0.251	0.427	0.910	1.58	4.58	1.30	1.44	1.11	0.910	1.58	0.745	0.813
23	0.251	0.383	0.910	1.58	33.1	1.30	1.44	1.11	0.910	1.58	0.745	0.813
24	0.251	0.539	0.910	1.58	12.3	1.30	1.44	1.11	0.910	1.44	0.745	0.745
25	0.251	2.83	0.910	1.58	7.45	1.30	1.44	1.11	0.910	1.44	0.676	0.676
26	0.251	1.30	0.910	1.58	7.45	1.30	1.44	1.11	0.910	1.44	0.676	0.608
27	0.251	0.813	7.08	1.58	5.60	1.30	1.44	1.11	0.910	1.44	0.676	0.608
28	0.251	0.745	34.9	1.58	5.09	1.30	1.44	1.11	0.910	1.44	0.676	0.676
29	0.251	0.608	10.1	1.58	-----	1.30	1.44	1.11	0.910	1.44	0.676	0.910
30	0.251	0.539	5.34	1.44	-----	1.44	1.30	1.11	0.910	1.30	0.676	0.813
31	0.251	-----	8.93	1.44	-----	1.44	-----	1.11	-----	1.30	0.676	-----
Maks.	0.339	5.34	63.6	47.9	63.6	62.3	1.44	1.30	83.3	56.8	1.30	0.910
Min.	0.251	0.251	0.539	1.44	1.30	1.20	1.20	1.11	0.910	0.676	0.676	0.608
Ortalama	0.264	0.497	2.90	3.91	3.92	2.91	1.36	1.18	1.52	4.46	0.977	0.664
LT/SN/Km2	1.27	2.39	13.9	18.8	18.8	14.0	6.54	5.68	7.31	21.4	4.69	3.19
AKIM mm.	3.39	6.19	37.3	50.3	45.5	37.5	16.9	15.2	18.9	57.4	12.6	8.26
MİL. M3	0.706	1.29	7.77	10.5	9.48	7.80	3.53	3.17	3.94	12.0	2.62	1.72

SU YILI (2006) YILLIK TOPLAM AKIM 64.53 MİLYON M3 310 MM. 9.8 LT/SN/Km2

02. Marmara Havzasi

D02A125 Sellimandira D. Gökçe Brj.Giris

YERİ : YALOVA İLİNDEN GÖKÇE BARAJINA GELİNİR.İSTASYON BARAJINMENBAINDAKİ ÜVEZPINARI MH GÜNEYİNDEDİR.
29°10'41" Doğu - 40°35'6" Kuzey

YAĞIŞ ALANI : 57,83 km2 **YAKLAŞIK KOT** : 91 m

GÖZLEM SÜRESİ : 01.10.1996 - 30.09.2006

ORTALAMA AKIMLAR : Gözlem süresinde 1.431 m3/sn. (9 Yıllık) 2006 Su yılında 1.554 m3/sn.

ANLIK EN ÇOK VE EN AZ AKIMLAR:

2006 Su yılında anlık ençok akım	:	31.0	m3/sn	05.03.2006
2006 Su yılında anlık enaz akım	:	0.064	m3/sn	01.10.2005
Gözlem süresinde anlık ençok akım	:	56.5	m3/sn	21.02.2000
Gözlem süresinde anlık enaz akım	:	0.010	m3/sn	21.08.2003

5. Anahtar Eğrisi (Seviyeler cm olarak)

Seviye	Akım	Seviye	Akım	Seviye	Akım	Seviye	Akım
16	0.090	48	2.0	94	10.2	150	30.0
20	0.165	56	3.0	110	15.0	180	45.0
24	0.280	64	4.1	120	18.0	190	50.0
28	0.440	74	5.6	130	22.0	200	55.0
37	0.980	84	8.4	140	26.0	210	60.0

Akımlar 01 Ekim 2005 'den 30 Eylül 2006' a kadar m3/sn olarak

Gün	Ekim	Kasım	Aralık	Ocak	Şubat	Mart	Nisan	Mayıs	Haziran	Temmuz	Ağustos	Eylül
01	0.103	0.833	0.790	5.32	1.25	12.6	2.28	0.700	0.247	0.220	0.185	0.168
02	0.150	0.355	0.610	3.25	1.30	10.8	2.03	0.655	0.247	0.220	0.185	0.168
03	0.247	0.247	0.700	2.28	1.30	18.1	1.95	0.610	0.247	0.203	0.185	0.168
04	0.150	0.410	0.575	1.87	1.40	10.4	1.87	0.575	0.220	0.203	0.185	0.168
05	0.103	0.575	0.508	1.40	1.50	6.80	1.60	0.575	0.220	0.185	0.185	0.168
06	0.064	0.383	0.475	1.20	1.50	8.60	1.40	0.540	0.247	0.185	0.185	0.168
07	0.064	0.508	0.443	1.35	1.35	8.82	1.35	0.540	0.273	0.185	0.185	0.168
08	0.064	0.383	0.383	2.12	1.40	8.20	1.35	0.508	0.273	0.185	0.185	0.168
09	0.064	0.247	0.508	2.90	1.20	5.48	1.30	0.508	0.383	0.185	0.185	0.168
10	0.064	0.203	0.410	2.12	2.28	4.16	1.25	0.475	0.960	0.185	0.185	0.168
11	0.077	0.150	0.443	1.60	12.3	4.30	1.14	0.475	0.355	0.185	0.185	0.168
12	0.115	0.133	0.443	1.40	5.32	9.92	1.14	0.475	0.300	0.185	0.185	0.168
13	0.090	0.133	0.443	1.60	3.48	9.48	1.08	0.443	0.410	0.185	0.185	0.168
14	0.103	0.383	0.443	1.78	2.51	8.60	1.08	0.410	0.475	0.185	0.185	0.168
15	0.090	1.40	0.410	1.50	2.03	6.28	0.960	0.410	0.355	0.185	0.185	0.168
16	0.185	0.833	0.475	1.30	1.70	4.72	0.960	0.383	0.300	0.185	0.185	0.150
17	0.220	0.540	0.610	1.20	1.60	3.74	0.960	0.383	0.273	0.185	0.185	0.150
18	0.150	0.875	1.02	1.02	3.48	3.37	0.918	0.443	0.273	0.185	0.185	0.150
19	0.103	1.30	2.59	4.02	6.28	3.48	0.875	0.355	0.220	0.185	0.185	0.150
20	0.150	4.16	1.87	5.64	7.60	3.37	0.875	0.328	0.220	0.185	0.185	0.150
21	0.103	2.90	1.40	3.25	8.20	3.60	0.875	0.328	0.220	0.185	0.185	0.150
22	0.090	1.35	1.20	2.36	8.20	4.44	0.875	0.355	0.220	0.185	0.185	0.133
23	0.077	1.14	1.08	2.12	8.20	5.16	0.875	0.328	0.300	0.185	0.185	0.133
24	0.077	2.59	0.960	1.78	7.80	5.48	0.833	0.355	0.203	0.185	0.185	0.133
25	0.077	5.96	0.833	1.60	9.70	4.30	0.833	0.300	0.220	0.185	0.185	0.133
26	0.090	6.80	0.875	1.40	16.0	3.37	0.790	0.300	0.220	0.185	0.185	0.133
27	0.090	3.48	1.30	1.30	15.7	3.13	0.745	0.300	0.220	0.185	0.185	0.115
28	0.103	2.20	4.44	1.14	11.0	2.90	0.745	0.273	0.410	0.185	0.185	0.115
29	0.103	1.40	6.60	1.02	-----	3.02	0.745	0.273	0.273	0.185	0.185	0.115
30	0.355	1.02	5.48	1.02	-----	3.02	0.745	0.273	0.247	0.185	0.185	0.115
31	1.02	-----	8.20	1.14	-----	2.51	-----	0.247	-----	0.185	0.185	-----
Maks.	1.40	12.1	15.4	11.9	21.1	31.0	2.59	0.745	2.36	0.247	0.185	0.168
Min.	0.064	0.103	0.355	0.960	1.14	2.36	0.700	0.247	0.185	0.185	0.168	0.115
Ortalama	0.146	1.43	1.50	2.03	5.20	6.20	1.15	0.423	0.301	0.188	0.185	0.152
LT/SN/Km2	2.53	24.7	25.9	35.1	89.9	107.	19.8	7.32	5.21	3.26	3.20	2.62
AKIM mm.	6.78	64.1	69.5	94.1	218.	287.	51.4	19.6	13.5	8.73	8.57	6.79
MİL. M3	0.392	3.71	4.02	5.44	12.6	16.6	2.97	1.13	0.780	0.505	0.496	0.393

SU YILI (2006) YILLIK TOPLAM AKIM 49.04 MİLYON M3 848 MM. 26.9 LT/SN/Km2

02. Marmara Havzasi

D02A126 Suludere Ihsaniye

YERİ : **BOYALICA-KARAMÜRSEL YOLUNDAN YAKLAŞIK 30 KM.SONRA İHSANİYEKÖYÜNE VARILIR.İSTASYON İHSANİYE KÖYÜNÜN 1.5 KM.KUZEYİNDE**
29°35'58" Doğu - 40°37'58" Kuzey

YAĞIŞ ALANI : **38,04 km2** **YAKLAŞIK KOT : 188 m**

GÖZLEM SÜRESİ : **01.10.1996 - 30.09.2006**

ORTALAMA AKIMLAR : **Gözlem süresinde 0.593 m3/sn. (7 Yıllık) 2006 Su yılında 0.652 m3/sn.**

ANLIK EN ÇOK VE EN AZ AKIMLAR:

2006 Su yılında anlık ençok akım	**:**	**11.8**	**m3/sn**	**11.02.2006**
2006 Su yılında anlık enaz akım	**:**	**0.013**	**m3/sn**	**11.08.2006**
Gözlem süresinde anlık ençok akım	**:**	**15.3**	**m3/sn**	**10.03.2000**
Gözlem süresinde anlık enaz akım	**:**	**0.013**	**m3/sn**	**30.08.2005**

3. Anahtar Eğrisi (Seviyeler cm olarak)

Seviye	Akım	Seviye	Akım	Seviye	Akım	Seviye	Akım
5	0.014	15	0.315	30	1.6	90	10.3
7	0.037	17	0.435	42	3.1	100	12.0
9	0.076	19	0.575	58	5.4	110	13.6
11	0.137	21	0.720	72	7.6	120	15.3
13	0.215	23	0.880	82	9.2	130	16.4

Akımlar 01 Ekim 2005 'den 30 Eylül 2006' a kadar m3/sn olarak

Gün	Ekim	Kasım	Aralık	Ocak	Şubat	Mart	Nisan	Mayıs	Haziran	Temmuz	Ağustos	Eylül
01	0.100	0.260	0.450	0.950	1.15	2.87	1.25	0.450	0.170	0.100	0.052	0.036
02	0.100	0.170	0.385	0.760	1.36	2.33	1.25	0.450	0.170	0.100	0.052	0.036
03	0.130	0.130	0.385	0.680	1.36	2.87	1.25	0.450	0.170	0.100	0.052	0.036
04	0.100	0.130	0.320	0.680	1.36	2.33	1.15	0.450	0.130	0.100	0.052	0.036
05	0.100	0.260	0.260	0.600	1.36	2.05	1.05	0.450	0.130	0.074	0.052	0.036
06	0.100	0.260	0.260	0.520	1.25	1.90	0.840	0.450	0.130	0.074	0.052	0.036
07	0.074	0.385	0.260	0.520	1.25	2.05	0.840	0.450	0.130	0.074	0.052	0.036
08	0.074	0.170	0.260	0.680	1.25	2.33	0.840	0.450	0.130	0.074	0.052	0.036
09	0.074	0.170	0.320	1.47	1.25	2.19	0.840	0.450	0.170	0.074	0.052	0.036
10	0.074	0.170	0.260	0.950	3.10	2.33	0.840	0.385	0.170	0.074	0.052	0.036
11	0.074	0.130	0.320	0.840	4.70	3.10	0.840	0.320	0.170	0.074	0.036	0.036
12	0.074	0.100	0.320	0.840	2.33	3.25	0.760	0.320	0.170	0.074	0.023	0.036
13	0.074	0.100	0.320	1.61	1.90	2.61	0.680	0.320	0.210	0.074	0.023	0.036
14	0.074	0.100	0.320	1.15	1.75	2.75	0.680	0.320	0.260	0.074	0.023	0.036
15	0.074	0.450	0.260	1.15	1.61	2.98	0.680	0.320	0.210	0.074	0.023	0.036
16	0.074	0.385	0.450	1.05	1.47	2.75	0.680	0.320	0.170	0.074	0.023	0.036
17	0.074	0.170	0.680	1.05	1.47	2.75	0.680	0.320	0.170	0.074	0.023	0.036
18	0.074	0.260	0.600	0.840	3.40	2.05	0.680	0.320	0.170	0.074	0.023	0.036
19	0.074	0.320	1.05	1.15	3.40	1.90	0.680	0.320	0.130	0.074	0.023	0.036
20	0.074	1.36	0.840	1.25	3.25	1.90	0.600	0.320	0.130	0.074	0.023	0.036
21	0.074	1.25	0.760	0.950	2.98	1.90	0.600	0.260	0.130	0.074	0.023	0.052
22	0.052	0.680	0.600	0.950	2.87	1.90	0.600	0.210	0.130	0.074	0.023	0.074
23	0.052	0.680	0.600	1.05	2.87	1.90	0.600	0.210	0.130	0.074	0.023	0.052
24	0.052	1.25	0.450	0.950	2.75	1.90	0.600	0.210	0.130	0.074	0.023	0.052
25	0.052	1.05	0.520	0.950	2.87	1.90	0.520	0.210	0.100	0.074	0.023	0.100
26	0.052	1.61	0.600	0.950	3.70	1.47	0.450	0.210	0.100	0.074	0.023	0.100
27	0.052	0.760	1.75	0.950	3.25	1.47	0.450	0.210	0.100	0.074	0.023	0.052
28	0.052	0.520	2.33	0.760	2.87	1.36	0.450	0.210	0.130	0.052	0.023	0.036
29	0.052	0.600	1.61	0.760	-----	1.25	0.450	0.170	0.130	0.052	0.023	0.052
30	0.100	0.520	1.15	0.840	-----	1.25	0.450	0.170	0.170	0.052	0.036	0.074
31	0.260	-----	1.05	0.950	-----	1.25	-----	0.170	-----	0.052	0.036	-----
Maks.	0.450	2.98	2.75	2.75	11.8	4.42	1.25	0.450	0.680	0.130	0.052	0.680
Min.	0.052	0.100	0.260	0.520	0.950	0.950	0.450	0.170	0.074	0.052	0.013	0.023
Ortalama	0.081	0.480	0.637	0.929	2.29	2.16	0.743	0.319	0.151	0.075	0.034	0.045
LT/SN/Km2	2.13	12.6	16.7	24.4	60.2	56.7	19.5	8.37	3.98	1.96	0.884	1.20
AKIM mm.	5.71	32.7	44.8	65.4	146.	152.	50.6	22.4	10.3	5.25	2.37	3.10
MİL. M3	0.217	1.24	1.71	2.49	5.54	5.77	1.92	0.853	0.392	0.200	0.090	0.118

SU YILI (2006) YILLIK TOPLAM AKIM 20.54 MİLYON M3 540 MM. 17.1 LT/SN/Km2

02. Marmara Havzasi

D02A129 KARANLİK DERE Kiriklar

YERİ : **YENİCE İLÇESİNDE KIRIKLAR-ÇIRPILAR KÖY YOLUNUN 2.KM SİNDEKİ KARAYOLU KÖPRÜSÜNDEDİR**

27°17'55" Doğu - 39°46'23" Kuzey

YAĞIŞ ALANI : **68.40 km2** **YAKLAŞIK KOT : 220 m**

GÖZLEM SÜRESİ : **13.12.1995 - 30.09.2006**

ORTALAMA AKIMLAR : **Gözlem süresinde 0.701 m3/sn. (8 Yıllık) 2006 Su yılında 0.682 m3/sn.**

ANLIK EN ÇOK VE EN AZ AKIMLAR:

2006 Su yılında anlık ençok akım	:	**31.9**	**m3/sn**	**30.12.2005**
2006 Su yılında anlık enaz akım	:	**0.001**	**m3/sn**	**18.07.2006**
Gözlem süresinde anlık ençok akım	:	**53.9**	**m3/sn**	**30.01.2004**
Gözlem süresinde anlık enaz akım	:	**0.000**	**m3/sn**	**03.07.1997**

10. Anahtar Eğrisi (Seviyeler cm olarak)

Seviye	Akım	Seviye	Akım	Seviye	Akım	Seviye	Akım
10	0.000	25	0.000	80	3.2	240	62.0
13	0.000	28	0.001	100	8.1	270	76.0
16	0.000	34	0.014	130	18.0	300	89.0
19	0.000	40	0.060	160	30.0	420	140.
22	0.000	50	0.310	180	37.5		

Akımlar 01 Ekim 2005 'den 30 Eylül 2006' a kadar m3/sn olarak

Gün	Ekim	Kasım	Aralık	Ocak	Şubat	Mart	Nisan	Mayıs	Haziran	Temmuz	Ağustos	Eylül
01	0.005	0.014	0.092	2.49	0.370	2.49	0.351	0.278	0.078	0.006	KURU	KURU
02	0.025	0.014	0.069	1.24	0.415	1.72	0.351	0.278	0.078	0.006	KURU	KURU
03	0.040	0.014	0.057	0.820	0.415	4.80	0.351	0.278	0.078	0.033	KURU	KURU
04	0.025	0.014	0.046	0.685	0.415	2.65	0.351	0.278	0.078	0.020	KURU	KURU
05	0.014	0.014	0.039	0.550	0.460	1.72	0.310	0.278	0.060	0.014	KURU	KURU
06	0.014	0.014	0.032	0.550	1.34	1.34	0.310	0.245	0.060	0.010	KURU	KURU
07	0.010	0.014	0.027	0.460	0.820	7.50	0.278	0.245	0.050	0.006	KURU	KURU
08	0.006	0.014	0.080	0.370	0.685	11.3	0.278	0.245	0.050	0.006	KURU	KURU
09	0.006	0.014	0.069	0.335	0.505	3.73	0.278	0.245	0.050	0.005	KURU	KURU
10	0.010	0.014	0.039	0.335	2.65	2.21	0.278	0.213	0.060	0.003	KURU	KURU
11	0.014	0.014	0.032	0.335	13.6	1.92	0.278	0.213	0.050	0.003	KURU	KURU
12	0.014	0.014	0.027	0.370	3.20	2.77	0.278	0.213	0.050	0.002	KURU	KURU
13	0.014	0.014	0.115	0.370	1.56	2.49	0.278	0.180	0.050	0.002	KURU	KURU
14	0.014	0.014	0.168	0.335	1.05	3.06	0.310	0.180	0.078	0.001	KURU	KURU
15	0.014	0.014	0.168	0.300	0.820	2.35	0.310	0.180	0.060	0.001	KURU	KURU
16	0.014	0.025	0.222	0.300	0.618	1.57	0.278	0.155	0.050	KURU	KURU	KURU
17	0.014	0.050	0.222	0.261	0.550	1.14	0.278	0.155	0.040	KURU	KURU	KURU
18	0.014	0.130	0.885	0.222	1.87	1.14	0.278	0.155	0.033	KURU	KURU	KURU
19	0.014	0.351	0.820	4.60	2.80	1.46	0.278	0.155	0.033	KURU	KURU	KURU
20	0.014	0.433	0.415	3.40	11.3	1.57	0.278	0.155	0.025	KURU	KURU	KURU
21	0.014	0.130	0.300	1.15	7.50	1.14	0.278	0.130	0.025	KURU	KURU	KURU
22	0.014	0.078	0.222	0.753	5.07	0.720	0.278	0.130	0.020	KURU	KURU	KURU
23	0.010	0.556	0.195	0.950	3.80	0.638	0.278	0.113	0.020	KURU	KURU	KURU
24	0.010	2.63	0.142	0.685	4.20	0.597	0.278	0.113	0.014	KURU	KURU	KURU
25	0.010	5.20	0.115	0.550	18.0	0.515	0.245	0.113	0.010	KURU	KURU	KURU
26	0.010	0.753	0.142	0.505	12.4	0.515	0.245	0.095	0.010	KURU	KURU	KURU
27	0.010	2.34	0.168	0.415	6.69	0.474	0.245	0.095	0.010	KURU	KURU	KURU
28	0.010	0.370	1.05	0.370	3.80	0.433	0.245	0.095	0.010	KURU	KURU	KURU
29	0.010	0.505	2.80	0.370	-----	0.392	0.278	0.078	0.010	KURU	KURU	0.988
30	0.020	0.168	4.40	0.335	-----	0.392	0.278	0.078	0.010	KURU	KURU	0.370
31	0.020	-----	7.77	0.335	-----	0.351	-----	0.078	-----	KURU	KURU	-----
Maks.	0.095	14.3	31.9	4.60	18.0	21.6	0.433	0.278	0.180	0.113	0.006	4.30
Min.	0.003	0.014	0.027	0.222	0.370	0.310	0.155	0.020	0.006	0.001	0.001	0.001
Ortalama	0.014	0.464	0.675	0.798	3.82	2.10	0.288	0.176	0.042	0.004	KURU	0.045
LT/SN/Km2	0.204	6.79	9.87	11.7	55.8	30.7	4.20	2.57	0.609	0.056	0.000	0.662
AKIM mm.	0.547	17.6	26.4	31.3	135.	82.2	10.9	6.87	1.58	0.149	0.000	1.72
MİL. M3	0.037	1.20	1.81	2.14	9.24	5.62	0.745	0.470	0.108	0.010	0.000	0.117

SU YILI (2006) YILLIK TOPLAM AKIM 21.50 MİLYON M3 314 MM. 10.0 LT/SN/Km2

02. Marmara Havzasi

D02A132 KOCAÇAY DERESİ Kumarlar

YERİ : **ÇAN-KUMARLAR KÖYÜ İÇINDEKI KÖPRÜNÜN 100 M. MEMBA TARAFINDADIR.**
26°49'51" Doğu - 40°2'21" Kuzey

YAĞIŞ ALANI : **40.30 km2** **YAKLAŞIK KOT : 185 m**

GÖZLEM SÜRESİ : **10.03.1999 - 30.09.2006**

ORTALAMA AKIMLAR : **Gözlem süresinde 0.497 m3/sn. (4 Yıllık) 2006 Su yılında 0.497 m3/sn.**

ANLIK EN ÇOK VE EN AZ AKIMLAR:

2006 Su yılında anlık ençok akım	**:**	**17.3**	**m3/sn**	**11.03.2006**
2006 Su yılında anlık enaz akım	**:**	**0.000**	**m3/sn**	**01.10.2005**
Gözlem süresinde anlık ençok akım	**:**	**21.8**	**m3/sn**	**25.12.2001**
Gözlem süresinde anlık enaz akım	**:**	**0.000**	**m3/sn**	**01.10.2000**

Akımlar 01 Ekim 2005 'den 30 Eylül 2006' a kadar m3/sn olarak

Gün	Ekim	Kasım	Aralık	Ocak	Şubat	Mart	Nisan	Mayıs	Haziran	Temmuz	Ağustos	Eylül
01	KURU	KURU	0.560	1.10	1.65	1.40	0.380	0.037	0.003	0.003	0.003	KURU
02	KURU	KURU	0.440	0.640	2.11	1.00	0.320	0.037	0.003	0.003	0.003	KURU
03	KURU	KURU	0.385	0.500	2.11	1.10	0.260	0.037	0.003	0.010	0.003	KURU
04	KURU	KURU	0.290	0.330	2.00	0.800	0.215	0.037	0.003	0.005	0.003	KURU
05	KURU	KURU	0.290	0.330	2.11	0.725	0.170	0.037	0.003	0.003	0.003	KURU
06	KURU	KURU	0.205	0.330	3.64	0.725	0.170	0.037	0.003	0.003	0.003	KURU
07	KURU	KURU	0.205	0.330	2.11	2.44	0.134	0.037	0.003	0.003	0.003	KURU
08	KURU	KURU	0.205	0.290	1.65	4.30	0.134	0.037	0.003	0.003	0.003	KURU
09	KURU	KURU	0.290	0.290	1.10	2.55	0.134	0.037	0.002	0.003	0.002	KURU
10	KURU	KURU	0.205	0.290	2.86	1.89	0.098	0.037	0.002	0.003	0.002	KURU
11	KURU	KURU	0.205	0.330	5.10	3.64	0.098	0.037	0.002	0.003	0.002	KURU
12	KURU	KURU	0.205	0.500	2.86	4.70	0.098	0.076	0.002	0.003	0.002	KURU
13	KURU	KURU	0.160	0.900	2.00	3.33	0.076	0.076	0.002	0.003	0.002	KURU
14	KURU	KURU	0.160	0.560	1.30	4.30	0.076	0.054	0.002	0.003	0.002	KURU
15	KURU	KURU	0.141	0.500	1.00	2.71	0.076	0.037	0.003	0.003	0.002	KURU
16	KURU	KURU	0.141	0.500	0.900	2.33	0.076	0.027	0.010	0.003	0.002	KURU
17	KURU	KURU	0.141	0.560	1.89	1.77	0.054	0.027	0.005	0.003	0.001	KURU
18	KURU	KURU	0.385	0.640	6.10	2.11	0.054	0.027	0.005	0.003	0.001	KURU
19	KURU	KURU	1.30	2.55	3.95	2.22	0.054	0.017	0.003	0.003	0.001	KURU
20	KURU	KURU	0.720	2.55	3.02	1.52	0.098	0.017	0.003	0.003	0.001	KURU
21	KURU	KURU	0.560	1.30	2.11	0.900	0.076	0.017	0.003	0.003	0.001	KURU
22	KURU	KURU	0.385	1.00	1.30	0.800	0.054	0.017	0.003	0.003	0.001	KURU
23	KURU	0.106	0.330	1.65	0.900	0.725	0.054	0.010	0.003	0.003	0.001	KURU
24	KURU	1.00	0.290	1.52	0.725	1.00	0.037	0.010	0.003	0.003	0.001	0.002
25	KURU	3.64	0.290	1.65	6.10	0.800	0.037	0.010	0.003	0.003	0.001	0.001
26	KURU	3.02	0.290	1.52	4.90	0.650	0.037	0.010	0.003	0.003	0.001	KURU
27	KURU	2.22	0.290	0.800	3.17	0.575	0.037	0.005	0.003	0.003	0.001	KURU
28	KURU	1.65	0.290	0.575	2.11	0.575	0.037	0.005	0.003	0.003	0.003	KURU
29	KURU	1.20	0.560	0.650	-----	0.575	0.037	0.005	0.003	0.003	0.001	KURU
30	KURU	0.720	0.500	0.725	-----	0.440	0.037	0.003	0.003	0.003	KURU	KURU
31	KURU	-----	2.55	1.20	-----	0.440	-----	0.003	-----	0.003	KURU	-----
Maks.	KURU	7.86	7.42	7.86	13.8	17.3	0.380	0.440	0.037	0.017	0.003	0.054
Min.	KURU	KURU	0.141	0.290	0.725	0.440	0.037	0.003	0.002	0.003	KURU	KURU
Ortalama	KURU	0.452	0.418	0.858	2.53	1.71	0.107	0.028	0.003	0.003	0.002	0.000
LT/SN/Km2	0.000	11.2	10.4	21.3	62.7	42.5	2.66	0.688	0.079	0.082	0.044	0.002
AKIM mm.	0.000	29.1	27.8	57.0	152.	114.	6.90	1.84	0.204	0.219	0.118	0.006
MİL. M3	0.000	1.17	1.12	2.30	6.11	4.58	0.278	0.074	0.008	0.009	0.005	0.000

SU YILI (2006) YILLIK TOPLAM AKIM 15.65 MİLYON M3 388 MM. 12.3 LT/SN/Km2

02. Marmara Havzasi

D02A133 Yagcidere Semetler

YERİ : **ORHANGAZİ-İZNİK KARAYOLUNDAN BOYALICA BELDESİNE VARILIRSOLA DÖNÜLÜR.15 KM.SONRA VALİDE KÖPRÜYÜ GEÇMEDEN SOLA DÖNÜ-**
29°29'13" Doğu - 40°36'54" Kuzey

YAĞIŞ ALANI : **17,56 km2** **YAKLAŞIK KOT : 104 m**

GÖZLEM SÜRESİ : **01.10.1997 - 30.09.2006**

ORTALAMA AKIMLAR : **Gözlem süresinde 0.209 m3/sn. (8 Yıllık) 2006 Su yılında 0.274 m3/sn.**

ANLIK EN ÇOK VE EN AZ AKIMLAR:

2006 Su yılında anlık ençok akım	:	**20.3**	**m3/sn**	**11.02.2006**
2006 Su yılında anlık enaz akım	:	**0.000**	**m3/sn**	**27.07.2006**
Gözlem süresinde anlık ençok akım	:	**20.3**	**m3/sn**	**11.02.2006**
Gözlem süresinde anlık enaz akım	:	**0.000**	**m3/sn**	**12.08.1999**

7. Anahtar Eğrisi (Seviyeler cm olarak)

Seviye	Akım	Seviye	Akım	Seviye	Akım	Seviye	Akım
22	0.000	35	0.230	70	2.8	120	10.3
24	0.006	42	0.560	80	4.0	130	12.1
26	0.020	52	1.2	90	5.3	140	13.5
28	0.050	54	1.4	100	6.8	150	15.3
30	0.087	60	1.9	110	8.5	160	17.7

Akımlar 01 Ekim 2005 'den 30 Eylül 2006' a kadar m3/sn olarak

Gün	Ekim	Kasım	Aralık	Ocak	Şubat	Mart	Nisan	Mayıs	Haziran	Temmuz	Ağustos	Eylül
01	0.041	0.155	0.155	0.345	0.400	0.640	0.290	0.110	0.054	0.019	KURU	KURU
02	0.026	0.019	0.078	0.245	0.400	0.580	0.290	0.110	0.054	0.019	KURU	KURU
03	0.067	0.009	0.078	0.155	0.400	1.74	0.290	0.110	0.054	0.019	KURU	KURU
04	0.067	0.155	0.054	0.155	0.400	0.910	0.245	0.110	0.054	0.019	KURU	KURU
05	0.041	0.110	0.029	0.110	0.400	0.640	0.200	0.110	0.054	0.019	KURU	KURU
06	0.026	0.110	0.019	0.078	0.400	0.580	0.200	0.110	0.054	0.019	KURU	KURU
07	0.026	0.245	0.019	0.078	0.400	0.730	0.200	0.110	0.054	0.019	KURU	KURU
08	0.026	0.155	0.019	0.200	0.345	1.46	0.200	0.110	0.054	0.019	KURU	KURU
09	0.026	0.078	0.029	1.09	0.400	1.28	0.245	0.110	0.054	0.019	KURU	KURU
10	0.026	0.054	0.029	0.400	4.00	1.09	0.200	0.110	0.029	0.019	KURU	KURU
11	0.026	0.054	0.029	0.345	7.44	1.56	0.200	0.078	0.029	0.009	KURU	KURU
12	0.026	0.029	0.029	0.245	1.93	3.35	0.200	0.078	0.029	0.009	KURU	KURU
13	0.026	0.029	0.029	0.245	1.37	1.19	0.200	0.110	0.078	0.009	KURU	KURU
14	0.026	0.054	0.019	0.245	1.19	0.910	0.200	0.110	0.054	0.009	KURU	KURU
15	0.026	0.200	0.019	0.200	1.00	1.00	0.200	0.110	0.029	0.009	KURU	KURU
16	0.026	0.155	0.054	0.155	0.820	0.910	0.200	0.110	0.029	0.009	KURU	KURU
17	0.026	0.078	0.200	0.110	0.730	0.820	0.200	0.110	0.029	0.009	KURU	KURU
18	0.041	0.200	0.078	0.110	1.84	0.640	0.200	0.054	0.029	0.009	KURU	KURU
19	0.041	0.460	0.520	1.00	1.93	0.730	0.200	0.054	0.029	0.009	KURU	KURU
20	0.041	1.37	0.345	1.37	1.84	0.640	0.200	0.054	0.029	0.009	KURU	KURU
21	0.041	0.820	0.200	0.640	1.37	0.580	0.200	0.054	0.029	0.005	KURU	KURU
22	0.026	0.290	0.110	0.520	1.09	0.520	0.200	0.054	0.029	0.005	KURU	KURU
23	0.026	0.520	0.110	0.460	0.820	0.520	0.155	0.054	0.029	0.005	KURU	KURU
24	0.026	1.56	0.110	0.400	0.640	0.460	0.155	0.054	0.029	0.005	KURU	KURU
25	0.026	1.00	0.110	0.400	0.640	0.460	0.155	0.054	0.029	0.005	KURU	KURU
26	0.026	1.09	0.290	0.345	1.09	0.460	0.110	0.054	0.029	0.005	KURU	KURU
27	0.026	0.580	0.520	0.290	1.28	0.460	0.110	0.054	0.029	KURU	KURU	KURU
28	0.026	0.345	1.19	0.290	0.820	0.400	0.110	0.054	0.029	KURU	KURU	KURU
29	0.026	0.245	0.640	0.290	-----	0.290	0.110	0.054	0.029	KURU	KURU	KURU
30	0.041	0.245	0.345	0.245	-----	0.290	0.110	0.054	0.029	KURU	KURU	KURU
31	0.204	-----	0.400	0.345	-----	0.290	-----	0.054	-----	KURU	KURU	-----
Maks.	0.518	2.83	1.37	5.90	20.3	9.42	0.290	0.200	0.290	0.019	KURU	0.005
Min.	0.026	0.009	0.019	0.078	0.345	0.200	0.110	0.054	0.019	KURU	KURU	KURU
Ortalama	0.038	0.347	0.189	0.358	1.26	0.843	0.193	0.083	0.039	0.010	KURU	KURU
LT/SN/Km2	2.15	19.8	10.8	20.4	72.0	48.0	11.0	4.71	2.22	0.569	0.000	0.000
AKIM mm.	5.76	51.2	28.8	54.6	174.	129.	28.4	12.6	5.75	1.53	0.000	0.000
MİL. M3	0.101	0.900	0.506	0.960	3.06	2.26	0.499	0.221	0.101	0.027	0.000	0.000

SU YILI (2006) YILLIK TOPLAM AKIM 8.64 MİLYON M3 492 MM. 15.6 LT/SN/Km2

02. Marmara Havzasi

D02A134 Karadere Karadereköyü

YERİ : **ORHANGAZİ-İZNİK KARAYOLUNDAN BOYALICA BELDESİNE VARILIRSOLA DÖNÜLÜR.15 KM.SONRA VALİDE KÖPRÜYÜ GEÇMEDEN SOLA DÖNÜ-**
29°28'29" Doğu - 40°38'0" Kuzey

YAĞIŞ ALANI : **22,39 km2** **YAKLAŞIK KOT : 71 m**

GÖZLEM SÜRESİ : **01.10.1997 - 30.09.2006**

ORTALAMA AKIMLAR : **Gözlem süresinde 0.214 m3/sn. (8 Yıllık) 2006 Su yılında 0.245 m3/sn.**

ANLIK EN ÇOK VE EN AZ AKIMLAR:

2006 Su yılında anlık ençok akım	**:**	**22.1**	**m3/sn**	**11.02.2006**
2006 Su yılında anlık enaz akım	**:**	**0.000**	**m3/sn**	**01.10.2005**
Gözlem süresinde anlık ençok akım	**:**	**29.1**	**m3/sn**	**25.12.2001**
Gözlem süresinde anlık enaz akım	**:**	**0.000**	**m3/sn**	**17.08.1999**

1. Anahtar Eğrisi (Seviyeler cm olarak)

Seviye	Akım	Seviye	Akım	Seviye	Akım	Seviye	Akım
10	0.000	25	0.066	80	2.4	220	21.2
13	0.000	29	0.120	140	8.1	240	25.7
16	0.000	35	0.240	160	10.7	260	29.9
19	0.010	42	0.440	180	13.8	280	34.4
22	0.033	52	0.860	200	17.3	300	39.8

Akımlar 01 Ekim 2005 'den 30 Eylül 2006' a kadar m3/sn olarak

Gün	Ekim	Kasım	Aralık	Ocak	Şubat	Mart	Nisan	Mayıs	Haziran	Temmuz	Ağustos	Eylül
01	KURU	0.162	0.138	0.374	0.475	0.860	0.276	0.114	0.006	0.001	0.001	0.001
02	KURU	0.073	0.090	0.243	0.510	0.660	0.276	0.114	0.001	0.001	0.001	0.001
03	KURU	0.073	0.090	0.186	0.475	1.50	0.276	0.114	0.001	0.001	0.001	0.001
04	KURU	0.090	0.090	0.138	0.545	0.860	0.276	0.114	0.001	0.001	0.001	0.001
05	KURU	0.090	0.073	0.114	0.510	0.660	0.210	0.114	0.001	0.001	0.001	0.001
06	KURU	0.090	0.073	0.090	0.700	0.545	0.210	0.114	0.001	0.001	0.001	0.001
07	KURU	0.090	0.073	0.090	0.620	0.660	0.210	0.114	0.001	0.001	0.001	0.001
08	KURU	0.090	0.073	0.341	0.580	1.67	0.210	0.114	0.001	0.001	0.001	0.001
09	KURU	0.073	0.057	1.22	0.660	1.45	0.210	0.114	0.006	0.001	0.001	0.001
10	KURU	0.073	0.040	0.475	2.48	1.01	0.210	0.114	0.006	0.001	0.001	0.001
11	KURU	0.057	0.040	0.341	6.30	1.15	0.210	0.073	0.010	0.001	0.001	0.001
12	KURU	0.025	0.040	0.276	1.73	2.18	0.210	0.073	0.010	0.001	0.001	0.001
13	KURU	0.025	0.040	0.276	1.39	1.22	0.186	0.090	0.010	0.001	0.001	0.001
14	KURU	0.025	0.040	0.276	1.05	1.05	0.186	0.090	0.025	0.001	0.001	0.001
15	KURU	0.057	0.040	0.276	0.908	1.10	0.186	0.090	0.040	0.001	0.001	0.001
16	KURU	0.114	0.073	0.210	0.800	0.740	0.186	0.073	0.025	0.001	0.001	0.001
17	KURU	0.073	0.309	0.138	0.660	0.700	0.138	0.073	0.025	0.001	0.001	0.001
18	KURU	0.073	0.162	0.138	1.28	0.620	0.138	0.057	0.010	0.001	0.001	0.001
19	KURU	0.162	0.908	0.510	1.62	0.620	0.138	0.057	0.006	0.001	0.001	0.001
20	0.057	0.580	0.475	1.05	1.67	0.510	0.138	0.040	0.006	0.001	0.001	0.001
21	0.073	0.580	0.276	0.545	1.39	0.475	0.138	0.040	0.001	0.001	0.001	0.001
22	0.040	0.210	0.186	0.440	1.10	0.440	0.138	0.040	0.001	0.001	0.001	0.001
23	0.025	0.186	0.162	0.407	0.908	0.374	0.138	0.025	0.001	0.001	0.001	0.001
24	0.010	0.545	0.186	0.374	0.860	0.374	0.138	0.025	0.001	0.001	0.001	0.001
25	0.010	0.440	0.186	0.374	0.908	0.374	0.138	0.025	0.001	0.001	0.001	0.073
26	0.010	0.475	0.374	0.374	1.45	0.374	0.114	0.010	0.001	0.001	0.001	0.138
27	0.010	0.276	0.580	0.309	1.45	0.374	0.114	0.010	0.001	0.001	0.001	0.114
28	0.025	0.186	0.800	0.276	0.957	0.309	0.090	0.010	0.001	0.001	0.001	0.114
29	0.025	0.162	0.545	0.276	-----	0.276	0.090	0.010	0.001	0.001	0.001	0.138
30	0.073	0.162	0.309	0.276	-----	0.276	0.114	0.006	0.001	0.001	0.001	0.162
31	0.186	-----	0.407	0.341	-----	0.276	-----	0.006	-----	0.001	0.001	-----
Maks.	0.341	1.62	1.10	3.04	22.1	4.37	0.276	0.114	0.073	0.040	0.001	0.800
Min.	KURU	0.025	0.040	0.090	0.374	0.276	0.090	0.006	0.001	0.001	0.001	0.001
Ortalama	0.018	0.177	0.224	0.347	1.21	0.764	0.176	0.067	0.007	0.001	0.001	0.025
LT/SN/Km2	0.784	7.92	9.99	15.5	54.2	34.1	7.88	2.97	0.301	0.045	0.045	1.14
AKIM mm.	2.10	20.5	26.8	41.5	131.	91.4	20.4	7.96	0.779	0.120	0.120	2.94
MİL. M3	0.047	0.459	0.599	0.929	2.94	2.05	0.457	0.178	0.017	0.003	0.003	0.066

SU YILI (2006) YILLIK TOPLAM AKIM 7.75 MİLYON M3 346 MM. 11.0 LT/SN/Km2

02. Marmara Havzasi

D02A135 Avcidere Avciköy

YERİ : **ORHANGAZİ-İZNİK KARAYOLUNDAN BOYALICA BELDESİNE VARILIRSOLA DÖNÜLÜR.15 KM.SONRA VALİDE KÖPRÜYÜ GEÇİP YALAKDERE BEL-**
29°34'54" Doğu - 40°36'9" Kuzey

YAĞIŞ ALANI : **36,80 km2** **YAKLAŞIK KOT : 138 m**

GÖZLEM SÜRESİ : **01.10.1997 - 30.09.2006**

ORTALAMA AKIMLAR : **Gözlem süresinde 0.522 m3/sn. (8 Yıllık) 2006 Su yılında 0.719 m3/sn.**

ANLIK EN ÇOK VE EN AZ AKIMLAR:

2006 Su yılında anlık ençok akım	**:**	**16.8**	**m3/sn**	**11.02.2006**
2006 Su yılında anlık enaz akım	**:**	**0.003**	**m3/sn**	**20.08.2006**
Gözlem süresinde anlık ençok akım	**:**	**32.2**	**m3/sn**	**25.12.2001**
Gözlem süresinde anlık enaz akım	**:**	**0.000**	**m3/sn**	**29.07.2000**

2. Anahtar Eğrisi (Seviyeler cm olarak)

Seviye	Akım	Seviye	Akım	Seviye	Akım	Seviye	Akım
10	0.000	26	0.290	76	7.8	130	24.5
13	0.000	33	0.760	80	9.0	140	28.0
16	0.001	40	1.4	90	11.5	160	35.0
19	0.033	50	2.7	100	14.7	170	39.0
22	0.113	64	5.1	120	21.0	200	50.0

Akımlar 01 Ekim 2005 'den 30 Eylül 2006' a kadar m3/sn olarak

Gün	Ekim	Kasım	Aralık	Ocak	Şubat	Mart	Nisan	Mayıs	Haziran	Temmuz	Ağustos	Eylül
01	0.097	0.350	0.710	1.77	1.23	2.83	0.710	0.350	0.120	0.097	0.034	0.073
02	0.097	0.260	0.530	1.50	1.50	2.25	0.710	0.350	0.120	0.097	0.050	0.097
03	0.213	0.260	0.440	1.10	1.63	3.50	0.620	0.350	0.120	0.097	0.050	0.120
04	0.097	0.350	0.440	0.950	1.77	2.60	0.620	0.260	0.097	0.120	0.050	0.097
05	0.050	0.950	0.350	0.710	1.77	1.90	0.620	0.260	0.097	0.120	0.034	0.073
06	0.050	0.620	0.350	0.530	1.50	1.63	0.530	0.260	0.097	0.120	0.034	0.073
07	0.034	0.950	0.260	0.440	1.23	1.77	0.440	0.260	0.120	0.120	0.034	0.050
08	0.034	0.440	0.260	0.440	1.23	2.08	0.440	0.260	0.120	0.120	0.050	0.050
09	0.034	0.260	0.350	0.800	0.950	1.90	0.440	0.260	0.120	0.120	0.050	0.050
10	0.034	0.167	0.260	0.710	2.25	1.77	0.350	0.260	0.213	0.120	0.050	0.050
11	0.034	0.120	0.350	0.620	5.80	3.50	0.350	0.213	0.167	0.120	0.050	0.050
12	0.097	0.097	0.440	0.620	2.83	5.30	0.350	0.213	0.120	0.120	0.034	0.097
13	0.073	0.097	0.440	0.950	1.90	3.05	0.350	0.260	0.213	0.120	0.018	0.073
14	0.050	0.120	0.440	0.950	1.63	2.83	0.350	0.213	0.213	0.120	0.018	0.050
15	0.050	0.440	0.350	0.800	1.37	3.50	0.350	0.213	0.167	0.120	0.018	0.050
16	0.050	0.350	0.620	0.710	1.23	3.05	0.260	0.213	0.167	0.097	0.018	0.050
17	0.097	0.213	1.23	0.620	1.23	2.83	0.260	0.213	0.167	0.097	0.018	0.050
18	0.097	0.530	0.800	0.620	2.83	2.25	0.260	0.213	0.120	0.097	0.018	0.050
19	0.073	0.710	1.50	1.50	4.80	1.90	0.260	0.213	0.120	0.097	0.012	0.097
20	0.120	2.25	1.10	2.25	5.30	1.77	0.260	0.167	0.120	0.073	0.006	0.097
21	0.097	1.77	0.950	1.50	4.80	1.50	0.260	0.167	0.097	0.073	0.006	0.213
22	0.097	0.950	0.710	1.50	4.15	1.50	0.260	0.167	0.097	0.050	0.006	0.213
23	0.073	1.37	0.620	1.37	3.50	1.50	0.213	0.120	0.097	0.050	0.006	0.213
24	0.050	5.30	0.620	1.10	3.50	1.50	0.213	0.120	0.097	0.050	0.006	0.213
25	0.050	3.50	0.530	0.950	3.50	1.37	0.260	0.120	0.073	0.050	0.012	0.260
26	0.050	2.60	0.620	0.800	3.72	1.10	0.350	0.120	0.073	0.050	0.012	0.167
27	0.073	1.23	1.63	0.800	3.28	0.950	0.350	0.120	0.073	0.034	0.006	0.097
28	0.073	0.800	5.80	0.620	4.80	0.950	0.350	0.167	0.097	0.034	0.018	0.097
29	0.073	0.800	4.80	0.620	-----	0.800	0.350	0.167	0.097	0.034	0.073	0.167
30	0.213	0.950	2.83	0.620	-----	0.800	0.350	0.120	0.097	0.034	0.050	0.260
31	0.530	-----	2.25	0.950	-----	0.800	-----	0.120	-----	0.034	0.050	-----
Maks.	1.23	7.87	7.07	4.37	16.8	8.61	0.710	0.350	0.440	0.167	0.097	1.23
Min.	0.034	0.097	0.260	0.350	0.950	0.710	0.167	0.120	0.073	0.018	0.003	0.034
Ortalama	0.092	0.960	1.05	0.949	2.69	2.10	0.383	0.210	0.123	0.087	0.029	0.110
LT/SN/Km2	2.51	26.1	28.6	25.8	73.0	57.0	10.4	5.71	3.35	2.35	0.781	2.99
AKIM mm.	6.71	67.6	76.5	69.1	177.	153.	27.0	15.3	8.68	6.30	2.09	7.74
MİL. M3	0.247	2.49	2.81	2.54	6.50	5.61	0.992	0.562	0.319	0.232	0.077	0.285

SU YILI (2006) YILLIK TOPLAM AKIM 22.66 MİLYON M3 616 MM. 19.5 LT/SN/Km2

02. Marmara Havzasi

D02A136 KAĞITHANE D. KAĞITHANE

YERİ : **KAĞITHANE İLÇESİ BELEDİYE BİNASI KARŞISINDAKİ KARAYOLU KÖPRÜSÜ ÜZERİNDEDİR. PAFTA :25.000 İST-F21-C3**
28°58'34" Doğu - 41°4'58" Kuzey

YAĞIŞ ALANI : **182,80 km2** **YAKLAŞIK KOT : 3 m**

GÖZLEM SÜRESİ : **02.07.1997 - 30.09.2006**

ORTALAMA AKIMLAR : **Gözlem süresinde 2.015 m3/sn. (11 Yıllık) 2006 Su yılında 2.454 m3/sn.**

ANLIK EN ÇOK VE EN AZ AKIMLAR:

2006 Su yılında anlık ençok akım	:	**110.**	**m3/sn**	**19.12.2005**
2006 Su yılında anlık enaz akım	:	**0.164**	**m3/sn**	**14.10.2005**
Gözlem süresinde anlık ençok akım	:	**119.**	**m3/sn**	**08.12.1997**
Gözlem süresinde anlık enaz akım	:	**0.040**	**m3/sn**	**02.09.2003**

5. Anahtar Eğrisi (Seviyeler cm olarak)

Seviye	Akım	Seviye	Akım	Seviye	Akım	Seviye	Akım
92	0.001	170	33.3	260	87.0	310	119.
100	0.040	190	45.1	270	93.0	320	127.
110	1.5	210	57.0	280	99.0	330	135.
130	10.7	230	69.0	290	105.	340	143.
150	21.8	250	81.0	300	112.	350	151.

Akımlar 01 Ekim 2005 'den 30 Eylül 2006' a kadar m3/sn olarak

Gün	Ekim	Kasım	Aralık	Ocak	Şubat	Mart	Nisan	Mayıs	Haziran	Temmuz	Ağustos	Eylül
01	0.288	2.73	1.04	1.27	3.55	4.37	5.60	0.288	0.810	0.810	0.580	0.288
02	0.350	0.810	1.27	1.27	6.11	4.37	3.96	0.350	0.580	0.580	0.580	0.580
03	0.580	0.810	3.14	1.04	6.62	5.19	2.32	0.580	0.580	0.580	0.350	0.288
04	0.350	0.580	1.91	1.04	6.62	3.96	1.91	0.580	0.580	0.350	0.580	0.288
05	0.288	0.810	1.50	1.04	6.11	3.96	1.50	0.580	0.350	0.580	0.350	0.288
06	0.288	0.810	1.27	1.27	15.7	3.55	1.27	0.580	0.288	0.580	0.350	0.350
07	0.350	0.580	1.04	1.91	10.2	7.13	1.27	0.810	0.288	0.580	0.350	0.288
08	0.350	0.580	1.04	4.37	6.11	20.7	1.50	0.810	0.350	0.350	0.810	0.350
09	0.350	0.580	0.810	5.19	5.60	15.1	1.91	0.810	0.810	0.580	0.810	0.350
10	1.04	0.580	0.810	11.3	14.6	8.15	2.32	0.810	0.350	0.350	0.580	0.580
11	0.580	0.580	0.580	14.0	22.9	5.19	1.91	0.810	0.350	0.350	0.580	0.350
12	0.350	0.580	0.580	12.9	12.4	5.19	1.91	0.580	0.580	0.350	0.580	0.580
13	0.226	0.810	0.810	10.2	9.68	4.78	1.50	0.580	0.350	0.580	0.350	0.580
14	0.164	1.04	0.810	6.11	5.60	7.64	1.50	0.580	0.288	0.350	0.350	0.350
15	0.288	1.04	1.04	3.96	3.96	13.5	1.50	0.580	0.350	0.350	0.350	0.350
16	0.350	1.04	1.04	2.73	2.73	6.62	1.27	0.810	0.580	0.580	0.350	0.350
17	0.350	1.04	1.04	1.50	3.96	6.11	1.27	1.04	0.350	0.580	0.350	0.288
18	0.350	1.27	9.17	1.04	12.9	5.60	0.810	1.27	0.350	0.350	0.350	0.288
19	0.350	1.50	46.3	3.55	11.3	5.19	0.350	1.50	0.350	0.350	0.350	0.288
20	0.350	2.73	49.8	10.2	7.64	4.78	0.288	1.91	0.288	0.350	0.350	0.288
21	0.350	1.91	14.6	4.78	4.78	4.37	0.350	1.50	0.288	0.580	0.580	0.226
22	0.226	1.50	2.32	3.14	4.37	3.96	0.580	1.27	0.350	0.580	0.580	0.226
23	0.226	1.50	1.50	2.32	4.37	3.55	0.810	1.04	0.350	0.350	0.580	5.60
24	0.288	2.32	3.55	1.91	4.37	4.78	0.810	1.27	0.810	0.288	0.810	4.37
25	0.288	4.37	4.37	1.91	5.60	6.11	0.810	1.27	0.810	0.288	0.580	1.50
26	0.350	5.19	3.14	1.91	7.13	5.60	1.04	1.04	0.580	0.350	0.580	0.810
27	0.350	3.96	2.32	1.91	12.4	5.60	0.810	0.810	0.580	0.810	0.350	0.580
28	0.288	1.91	1.91	1.50	6.11	5.19	0.350	0.810	0.580	0.580	0.810	0.288
29	0.288	1.27	1.50	1.50	-----	3.96	0.288	0.580	0.580	0.580	0.580	0.580
30	0.288	1.04	1.50	1.91	-----	5.19	0.226	0.580	0.810	0.580	0.350	0.288
31	1.27	-----	1.27	2.32	-----	6.11	-----	0.580	-----	0.580	0.350	-----
Maks.	13.5	6.62	110.	17.9	28.7	23.5	6.11	2.32	1.27	1.27	9.17	25.8
Min.	0.164	0.580	0.350	1.04	2.73	3.55	0.226	0.288	0.226	0.288	0.288	0.226
Ortalama	0.381	1.52	5.26	3.90	7.98	6.31	1.40	0.858	0.485	0.487	0.498	0.728
LT/SN/Km2	2.08	8.29	28.8	21.4	43.7	34.5	7.65	4.70	2.65	2.66	2.73	3.98
AKIM mm.	5.58	21.5	77.0	57.2	106.	92.4	19.8	12.6	6.88	7.14	7.30	10.3
MİL. M3	1.02	3.93	14.1	10.5	19.3	16.9	3.62	2.30	1.26	1.30	1.33	1.89

SU YILI (2006) YILLIK TOPLAM AKIM 77.45 MİLYON M3 424 MM. 13.4 LT/SN/Km2

02. Marmara Havzasi

D02A137 KURBAĞALI D. KADIKÖY

YERİ : KADIKÖY İLÇESİ HASANPAŞA İETT OTOBÜS GARAJI İÇİNDEKİ KÖPRÜDEDİR. PAFTA :25.000 BUR-G22-A1
29°2'31" Doğu - 40°59'39" Kuzey

YAĞIŞ ALANI : 40,80 km2 **YAKLAŞIK KOT** : 3 m

GÖZLEM SÜRESİ : 06.03.1997 - 30.09.2006

ORTALAMA AKIMLAR : Gözlem süresinde 1.196 m3/sn. (7 Yıllık) 2006 Su yılında 0.445 m3/sn.

ANLIK EN ÇOK VE EN AZ AKIMLAR:

2006 Su yılında anlık ençok akım	:	20.3	m3/sn	18.12.2005
2006 Su yılında anlık enaz akım	:	0.003	m3/sn	17.03.2006
Gözlem süresinde anlık ençok akım	:	54.6	m3/sn	08.10.2004
Gözlem süresinde anlık enaz akım	:	0.000	m3/sn	08.11.1998

3. Anahtar Eğrisi (Seviyeler cm olarak)

Seviye	Akım	Seviye	Akım	Seviye	Akım	Seviye	Akım
101	0.000	140	4.2	290	40.2	400	66.6
104	0.004	170	11.4	320	47.4	410	69.0
107	0.030	200	18.6	350	54.6	420	71.4
110	0.110	230	25.8	380	61.8	430	73.8
125	1.3	260	33.0	390	64.2	440	76.2

Akımlar 01 Ekim 2005 'den 30 Eylül 2006' a kadar m3/sn olarak

Gün	Ekim	Kasım	Aralık	Ocak	Şubat	Mart	Nisan	Mayıs	Haziran	Temmuz	Ağustos	Eylül
01	0.025	0.730	0.025	0.105	1.55	0.150	0.006	0.006	0.006	0.006	0.003	0.200
02	0.600	0.260	0.070	0.105	1.40	0.105	0.006	0.006	0.003	0.006	0.003	0.860
03	0.015	0.330	0.730	0.105	1.40	0.410	0.006	0.006	0.003	0.006	0.003	0.200
04	0.006	0.410	0.044	0.200	1.25	0.105	0.006	0.006	0.003	0.006	0.003	0.200
05	0.006	0.150	0.044	0.410	1.25	0.105	0.006	0.006	0.003	0.006	0.003	0.200
06	0.006	0.500	0.044	0.410	2.80	0.150	0.006	0.006	0.003	0.006	0.003	0.150
07	0.006	0.200	0.044	0.600	1.40	2.80	0.006	0.006	0.003	0.003	0.003	0.150
08	0.006	0.105	0.150	1.25	1.70	3.00	0.044	0.015	0.015	0.003	0.015	0.150
09	0.006	0.105	0.044	3.00	1.40	2.00	0.025	0.006	0.105	0.003	0.006	0.150
10	0.044	0.105	0.015	2.60	7.80	0.260	0.006	0.006	0.200	0.003	0.006	0.150
11	0.025	0.105	0.025	2.80	2.20	0.150	0.006	0.006	0.070	0.003	0.006	0.150
12	0.006	0.105	0.015	2.80	1.25	0.260	0.006	0.006	0.070	0.003	0.006	0.150
13	0.006	0.500	0.006	2.20	0.860	0.410	0.006	0.006	2.00	0.003	0.006	0.150
14	0.006	0.730	0.006	1.85	0.600	0.990	0.006	0.006	0.330	0.003	0.006	0.150
15	0.025	0.260	0.006	1.12	0.410	1.12	0.006	0.015	0.150	0.003	0.006	0.150
16	0.200	0.105	0.990	0.860	0.330	0.105	0.006	0.025	0.150	0.003	0.015	0.150
17	0.044	0.200	0.105	0.600	0.260	0.006	0.006	0.015	0.105	0.003	0.006	0.150
18	0.600	2.60	4.44	0.410	0.500	0.006	0.006	0.006	0.105	0.003	0.006	0.150
19	0.070	0.600	5.16	4.20	0.330	0.003	0.006	0.006	0.105	0.003	0.006	0.150
20	0.260	2.80	0.730	2.40	0.200	0.003	0.006	0.006	0.070	0.003	0.006	0.200
21	0.150	0.500	0.105	1.85	0.150	0.003	0.003	0.006	0.070	0.003	0.006	1.40
22	0.070	0.200	0.105	1.55	0.150	0.003	0.003	0.006	0.070	0.003	0.006	1.55
23	0.070	0.990	0.070	1.70	0.105	0.003	0.006	0.006	0.044	0.003	0.006	1.40
24	0.070	0.990	0.330	1.55	0.150	0.330	0.006	0.006	0.044	0.003	0.044	1.40
25	0.070	4.44	0.500	1.55	1.12	0.044	0.006	0.006	0.044	0.003	0.200	2.40
26	0.070	1.25	0.150	1.70	1.25	0.006	0.006	0.006	0.044	0.003	0.105	1.25
27	0.070	0.500	0.105	1.70	0.410	0.003	0.006	0.006	0.044	0.003	0.200	0.500
28	0.044	0.105	0.200	1.70	0.200	0.003	0.003	0.006	0.015	0.003	0.500	0.860
29	1.12	0.410	0.150	1.70	-----	0.003	0.150	0.006	0.015	0.003	0.105	2.20
30	1.55	0.070	0.105	1.55	-----	0.105	0.025	0.006	0.006	0.003	0.105	1.25
31	5.64	-----	1.25	1.55	-----	0.006	-----	0.006	-----	0.003	0.105	-----
Maks.	17.4	13.8	20.3	14.8	19.6	14.5	1.70	0.200	9.00	0.025	1.25	10.2
Min.	0.006	0.070	0.006	0.105	0.105	0.003	0.003	0.006	0.003	0.003	0.003	0.105
Ortalama	0.351	0.679	0.508	1.49	1.16	0.408	0.013	0.007	0.130	0.004	0.048	0.606
LT/SN/Km2	8.61	16.6	12.5	36.5	28.4	10.00	0.319	0.183	3.18	0.088	1.19	14.8
AKIM mm.	23.1	43.1	33.4	97.7	68.7	26.8	0.828	0.491	8.25	0.235	3.17	38.5
MİL. M3	0.941	1.76	1.36	3.99	2.80	1.09	0.034	0.020	0.337	0.010	0.130	1.57

SU YILI (2006) YILLIK TOPLAM AKIM 14.04 MİLYON M3 344 MM. 10.9 LT/SN/Km2

02. Marmara Havzasi

D02A138 GÖNEN ÇAYI Bayatlar

YERİ : **YENİCE-BAYATLAR KÖYÜNDEKİ AGONYA KÖPRÜSÜNÜN 500 M MEMBAINDAKI REGÜLATÖRDEDIR.**
27°19'34" Doğu - 39°50'3" Kuzey

YAĞIŞ ALANI : **650.02 km2** **YAKLAŞIK KOT : 180 m**

GÖZLEM SÜRESİ : **12.11.1999 - 30.09.2006**

ORTALAMA AKIMLAR : **Gözlem süresinde 9.674 m3/sn. (5 Yıllık) 2006 Su yılında 12.799 m3/sn.**

ANLIK EN ÇOK VE EN AZ AKIMLAR:

2006 Su yılında anlık ençok akım	:	**381.**	**m3/sn**	**25.11.2005**
2006 Su yılında anlık enaz akım	:	**0.030**	**m3/sn**	**20.08.2006**
Gözlem süresinde anlık ençok akım	:	**771.**	**m3/sn**	**18.02.2003**
Gözlem süresinde anlık enaz akım	:	**0.030**	**m3/sn**	**20.08.2006**

Akımlar 01 Ekim 2005 'den 30 Eylül 2006' a kadar m3/sn olarak

Gün	Ekim	Kasım	Aralık	Ocak	Şubat	Mart	Nisan	Mayıs	Haziran	Temmuz	Ağustos	Eylül
01	0.325	0.975	9.06	49.8	9.67	70.8	12.5	6.01	1.48	1.23	0.126	0.048
02	0.725	0.975	7.23	31.4	10.9	49.8	11.5	6.01	1.35	0.850	0.126	0.082
03	0.725	0.975	6.01	21.5	10.9	65.7	10.9	5.40	1.23	1.35	0.107	0.045
04	0.600	0.975	5.02	18.5	10.9	51.3	10.3	5.40	0.975	1.48	0.096	0.045
05	0.600	0.850	4.64	15.5	12.5	41.3	10.3	5.02	1.10	1.48	0.087	0.045
06	0.600	0.350	3.88	14.5	34.3	32.8	10.3	5.02	0.975	0.725	0.078	0.045
07	0.475	0.350	3.50	11.5	21.5	67.4	9.67	5.02	1.10	0.600	0.070	0.045
08	0.475	0.350	3.50	10.3	17.5	139.	9.67	4.64	1.60	0.350	0.062	0.045
09	0.475	0.350	4.64	9.06	13.5	72.5	10.3	4.64	2.74	0.300	0.055	0.045
10	0.475	0.350	3.88	9.06	52.7	52.7	9.67	4.64	2.74	0.230	0.048	0.045
11	0.600	0.350	3.50	9.06	166.	52.7	9.06	4.26	2.36	0.600	0.045	0.051
12	0.600	0.350	3.50	9.67	58.3	74.2	9.06	4.26	1.98	0.600	0.042	0.055
13	0.725	0.350	3.12	9.67	37.1	59.8	9.06	4.26	2.36	0.600	0.039	0.048
14	0.600	0.350	3.12	9.06	27.2	72.5	9.06	4.26	2.74	0.600	0.039	0.045
15	0.725	0.475	2.74	8.45	20.5	59.8	9.06	5.02	2.36	0.600	0.036	0.039
16	0.725	0.475	2.74	7.84	16.5	48.4	8.45	5.02	3.12	0.600	0.036	0.042
17	0.725	0.475	2.74	7.23	14.5	39.9	7.84	4.64	2.36	0.600	0.036	0.042
18	0.725	1.10	6.01	6.62	41.3	41.3	7.84	4.26	1.98	0.475	0.033	0.048
19	0.725	1.23	25.8	74.2	54.1	41.3	7.84	4.26	1.98	0.600	0.033	0.062
20	0.850	2.74	14.5	61.2	64.0	34.3	7.23	3.88	1.60	0.475	0.033	0.210
21	0.850	1.48	11.5	28.6	55.5	28.6	7.23	3.88	1.48	0.600	0.030	0.133
22	0.850	1.23	10.3	19.5	45.6	24.3	7.23	3.50	1.35	0.600	0.030	0.087
23	0.850	1.10	9.67	24.3	37.1	21.5	7.23	3.12	1.23	0.475	0.030	0.082
24	0.850	12.5	9.06	18.5	34.3	24.3	6.62	2.74	1.10	0.350	0.030	0.165
25	0.850	148.	9.06	15.5	135.	20.5	6.62	2.36	0.850	0.325	0.030	1.23
26	0.850	84.4	9.67	13.5	189.	19.5	6.62	2.36	0.725	0.325	0.030	1.10
27	0.850	51.3	10.3	10.9	123.	17.5	6.01	1.98	1.10	0.275	0.030	1.10
28	0.850	34.3	27.2	10.3	77.6	17.5	6.01	1.98	1.98	0.210	0.030	1.10
29	0.850	21.5	87.8	9.67	-----	15.5	6.01	1.98	1.60	0.165	0.030	6.62
30	0.850	13.5	69.1	9.06	-----	14.5	6.01	1.60	1.48	0.165	0.030	5.40
31	0.975	-----	87.8	9.06	-----	13.5	-----	1.48	-----	0.159	0.030	-----
Maks.	1.98	381.	156.	191.	316.	234.	12.5	6.01	3.50	1.98	0.146	37.1
Min.	0.325	0.350	2.74	6.01	9.06	10.9	3.50	0.975	0.300	0.133	0.030	0.030
Ortalama	0.708	12.8	14.9	18.2	49.7	44.7	8.51	3.96	1.70	0.580	0.050	0.605
LT/SN/Km2	1.09	19.7	22.9	27.9	76.4	68.7	13.1	6.10	2.62	0.893	0.077	0.931
AKIM mm.	2.92	51.0	61.2	74.8	185.	184.	33.9	16.3	6.78	2.39	0.207	2.41
MİL. M3	1.90	33.2	39.8	48.6	120.	120.	22.0	10.6	4.41	1.55	0.135	1.57

SU YILI (2006) YILLIK TOPLAM AKIM 403.77 MİLYON M3 621 MM. 19.7 LT/SN/Km2

02. Marmara Havzasi

D02A140 YEŞİL D. KALEDİBİ

YERİ : İSTANBUL-ŞİLE YOLU (ESKİ YOL)ÜZERİNDEKİ KALEDİBİ MEVKİİNDEDİR. PAFTA: 25.000 İST-F23-D4
29°30'53" Doğu - 41°7'16" Kuzey

YAĞIŞ ALANI : 63,00 km2 **YAKLAŞIK KOT** : 20 m

GÖZLEM SÜRESİ : 01.10.2001 - 30.09.2006

ORTALAMA AKIMLAR : Gözlem süresinde 1.389 m3/sn. (5 Yıllık) 2006 Su yılında 1.743 m3/sn.

ANLIK EN ÇOK VE EN AZ AKIMLAR:

2006 Su yılında anlık ençok akım	:	55.4	m3/sn	19.12.2005
2006 Su yılında anlık enaz akım	:	0.020	m3/sn	19.08.2006
Gözlem süresinde anlık ençok akım	:	64.9	m3/sn	18.12.2001
Gözlem süresinde anlık enaz akım	:	0.001	m3/sn	28.06.2004

2. Anahtar Eğrisi (Seviyeler cm olarak)

Seviye	Akım	Seviye	Akım	Seviye	Akım	Seviye	Akım
47	0.000	80	1.2	230	27.5	380	65.4
50	0.010	110	4.0	260	34.4	390	68.1
53	0.053	140	8.5	290	41.7	400	70.8
56	0.130	170	14.0	320	49.4	410	73.6
59	0.230	200	20.6	350	57.3	420	76.4

Akımlar 01 Ekim 2005 'den 30 Eylül 2006' a kadar m3/sn olarak

Gün	Ekim	Kasım	Aralık	Ocak	Şubat	Mart	Nisan	Mayıs	Haziran	Temmuz	Ağustos	Eylül
01	0.450	0.900	0.570	1.23	3.16	1.60	0.850	0.490	0.130	0.109	0.053	0.030
02	0.195	0.610	0.570	1.00	3.76	1.23	0.850	0.490	0.175	0.080	0.053	0.570
03	0.130	0.570	1.23	0.850	3.40	1.99	0.800	0.450	0.130	0.080	0.053	0.175
04	0.109	0.570	0.800	0.800	3.04	1.30	0.800	0.450	0.109	0.080	0.053	0.080
05	0.109	0.700	0.610	0.750	2.53	1.10	0.800	0.450	0.109	0.080	0.053	0.053
06	0.109	0.750	0.490	0.750	17.9	0.950	0.750	0.450	0.130	0.053	0.030	0.053
07	0.109	0.450	0.450	0.950	5.85	4.70	0.750	0.450	0.130	0.130	0.053	0.030
08	0.109	0.290	0.530	2.08	4.00	28.0	0.750	0.450	0.109	0.080	0.080	0.030
09	0.109	0.250	0.650	9.86	3.64	15.3	0.750	0.490	0.570	0.080	0.080	0.030
10	0.109	0.230	0.490	16.1	14.8	5.85	0.700	0.410	0.850	0.080	0.053	0.053
11	0.109	0.175	0.490	10.2	26.6	3.64	0.700	0.410	0.230	0.109	0.053	0.109
12	0.175	0.175	0.490	11.1	7.54	2.62	0.700	0.410	0.195	0.080	0.053	0.109
13	0.130	4.42	0.450	4.70	4.70	2.35	0.650	0.410	0.250	0.080	0.053	0.053
14	0.080	2.92	0.450	9.35	3.04	2.17	0.650	0.410	1.10	0.080	0.053	0.053
15	0.109	1.83	0.450	5.40	2.17	2.35	0.650	0.410	0.290	0.080	0.030	0.053
16	0.410	0.650	0.850	2.44	1.83	2.26	0.610	0.370	0.230	0.080	0.030	0.053
17	0.610	0.450	1.15	1.68	3.76	1.99	0.610	0.370	0.195	0.053	0.030	0.053
18	0.330	0.800	8.50	1.30	19.0	1.75	0.610	0.330	0.175	0.080	0.030	0.053
19	0.370	0.850	38.2	23.4	12.0	1.60	0.610	0.330	0.130	0.053	0.020	0.053
20	0.330	18.8	5.70	15.1	9.69	1.45	0.570	0.330	0.175	0.053	0.020	0.053
21	0.195	8.18	2.26	3.88	5.40	1.30	0.570	0.330	0.130	0.080	0.020	0.053
22	0.175	1.45	1.68	2.26	3.40	1.23	0.570	0.290	0.175	0.080	0.020	0.053
23	0.130	1.23	1.99	2.80	2.26	1.10	0.570	0.290	0.130	0.080	0.020	0.850
24	0.130	3.28	2.35	2.08	1.75	1.05	0.530	0.290	0.109	0.080	0.020	1.75
25	0.109	4.14	2.26	1.90	2.44	1.00	0.530	0.250	0.109	0.053	0.020	0.850
26	0.109	8.50	5.40	1.75	3.16	1.00	0.530	0.250	0.109	0.053	0.020	0.490
27	0.109	1.60	5.55	1.60	5.40	0.950	0.530	0.290	0.109	0.053	0.020	0.410
28	0.109	0.950	4.00	1.60	2.26	0.950	0.490	0.230	0.109	0.053	0.020	0.370
29	0.175	0.750	1.99	1.68	-----	0.900	0.490	0.230	0.109	0.053	0.030	0.370
30	0.650	0.650	1.30	1.83	-----	0.900	0.490	0.195	0.130	0.053	0.020	0.410
31	4.56	-----	1.83	2.26	-----	0.900	-----	0.195	-----	0.053	0.020	-----
Maks.	9.69	35.6	55.4	48.4	45.8	35.8	0.850	0.570	8.18	0.130	0.175	22.2
Min.	0.080	0.130	0.410	0.650	1.60	0.850	0.490	0.175	0.080	0.053	0.020	0.030
Ortalama	0.343	2.24	3.02	4.60	6.37	3.08	0.649	0.361	0.221	0.074	0.038	0.245
LT/SN/Km2	5.45	35.5	48.0	73.1	101.	48.9	10.3	5.73	3.51	1.17	0.595	3.89
AKIM mm.	14.6	92.1	129.	196.	245.	131.	26.7	15.4	9.09	3.14	1.59	10.1
MİL. M3	0.919	5.80	8.10	12.3	15.4	8.25	1.68	0.968	0.573	0.198	0.100	0.635

SU YILI (2006) YILLIK TOPLAM AKIM 54.92 MİLYON M3 872 MM. 27.7 LT/SN/Km2

02. Marmara Havzasi

D02A141 DEGİRMENDERE KOCAYAZI

YERİ : **KOCAYAZI-GECITAGZI YOLU 5.5 KMSINDEKI KOPRUDE MANSAPTADIR.E18B1**
27°15'15" Doğu - 41°59'20" Kuzey

YAĞIŞ ALANI : **44,20 km2** **YAKLAŞIK KOT : 428 m**

GÖZLEM SÜRESİ : **18.11.2002 – 30.09.2006**

ORTALAMA AKIMLAR : **Gözlem süresinde 0.479 m3/sn. (3 Yıllık) 2006 Su yılında 0.632 m3/sn.**

ANLIK EN ÇOK VE EN AZ AKIMLAR:

2006 Su yılında anlık ençok akım	:	**43.3**	**m3/sn**	**02.07.2006**
2006 Su yılında anlık enaz akım	:	**0.048**	**m3/sn**	**02.10.2005**
Gözlem süresinde anlık ençok akım	:	**43.3**	**m3/sn**	**02.07.2006**
Gözlem süresinde anlık enaz akım	:	**0.048**	**m3/sn**	**26.09.2005**

İstasyon için kullanılmış anahtar bulunamadı.

Akımlar 01 Ekim 2005 'den 30 Eylül 2006' a kadar m3/sn olarak

Gün	Ekim	Kasım	Aralık	Ocak	Şubat	Mart	Nisan	Mayıs	Haziran	Temmuz	Ağustos	Eylül
01	0.048	0.048	0.108	1.26	0.473	1.77	0.606	0.473	0.354	0.354	0.660	0.440
02	0.048	0.048	0.124	0.980	0.473	1.19	0.606	0.473	0.354	10.2	0.550	0.440
03	0.048	0.048	0.124	1.05	0.473	0.752	0.606	0.473	0.354	9.53	0.550	0.440
04	0.048	0.048	0.124	0.980	0.473	0.517	0.606	0.473	0.354	4.76	0.550	0.440
05	0.048	0.048	0.124	0.980	0.473	0.473	0.606	0.473	0.354	3.44	0.550	0.440
06	0.048	0.048	0.124	2.07	0.473	0.473	0.606	0.433	0.354	2.60	0.550	0.440
07	0.048	0.048	0.108	2.07	0.473	0.473	0.606	0.433	0.354	2.12	0.550	0.440
08	0.048	0.048	0.108	1.51	0.473	0.473	0.562	0.433	0.354	2.00	0.550	0.440
09	0.048	0.048	0.244	1.19	0.473	0.473	0.562	0.433	0.433	1.88	0.550	0.440
10	0.048	0.048	0.354	0.980	0.473	0.473	0.562	0.433	0.354	1.64	0.550	0.340
11	0.048	0.048	0.274	0.923	0.473	0.473	0.562	0.393	0.354	0.780	0.550	0.340
12	0.048	0.048	0.244	0.866	0.473	8.50	0.562	0.393	0.354	0.660	0.550	0.340
13	0.048	0.048	0.244	0.752	0.473	2.17	0.562	0.393	0.354	0.660	0.550	0.340
14	0.048	0.048	0.214	0.651	0.473	1.19	0.562	0.393	0.393	0.660	0.550	0.340
15	0.048	0.048	0.184	0.606	0.473	0.651	0.562	0.393	0.393	0.660	0.550	0.340
16	0.048	0.048	0.184	0.606	0.473	0.562	0.562	0.393	0.354	0.660	0.550	0.340
17	0.048	0.048	0.184	0.562	0.473	0.562	0.562	0.393	0.354	0.660	0.550	0.240
18	0.048	0.066	0.184	0.517	0.752	0.562	0.562	0.393	0.354	0.660	0.550	0.240
19	0.048	0.108	0.184	0.517	0.809	0.562	0.562	0.393	0.354	0.660	0.550	0.240
20	0.048	0.083	0.184	0.517	0.866	0.562	0.562	0.393	0.354	0.660	0.550	0.240
21	0.048	0.083	0.184	0.473	0.923	0.562	0.562	0.354	0.354	0.660	0.550	0.240
22	0.048	0.083	0.184	0.473	0.980	0.562	0.562	0.354	0.354	0.660	0.550	0.240
23	0.048	0.083	0.184	0.473	8.04	0.562	0.562	0.354	0.354	0.660	0.550	0.240
24	0.048	0.124	0.184	0.473	5.66	0.562	0.562	0.354	0.354	0.660	0.440	0.150
25	0.048	0.809	0.184	0.473	5.10	0.562	0.562	0.354	0.354	0.660	0.440	0.150
26	0.048	0.314	0.214	0.473	3.27	0.562	0.562	0.354	0.354	0.660	0.440	0.150
27	0.048	0.184	0.980	0.473	2.76	0.562	0.562	0.354	0.354	0.660	0.440	0.150
28	0.048	0.154	3.78	0.473	2.36	0.562	0.517	0.354	0.354	0.660	0.440	0.150
29	0.048	0.154	1.87	0.473	-----	0.562	0.517	0.354	0.354	0.660	0.440	0.150
30	0.048	0.124	1.68	0.473	-----	0.562	0.517	0.354	0.354	0.660	0.440	0.080
31	0.048	-----	1.59	0.473	-----	0.562	-----	0.354	-----	0.660	0.440	-----
Maks.	0.048	1.26	6.69	3.02	8.97	9.28	0.606	0.473	0.866	43.3	0.660	0.440
Min.	0.048	0.048	0.108	0.473	0.473	0.433	0.517	0.354	0.354	0.354	0.440	0.080
Ortalama	0.048	0.106	0.473	0.800	1.41	0.937	0.568	0.399	0.359	1.69	0.525	0.300
LT/SN/Km2	1.09	2.40	10.7	18.1	32.0	21.2	12.8	9.02	8.13	38.3	11.9	6.79
AKIM mm.	2.91	6.23	28.6	48.5	77.3	56.8	33.3	24.1	21.1	103.	31.8	17.6
MİL. M3	0.129	0.275	1.27	2.14	3.42	2.51	1.47	1.07	0.931	4.54	1.41	0.778

SU YILI (2006) YILLIK TOPLAM AKIM 19.94 MİLYON M3 451 MM. 14.3 LT/SN/Km2

02. Marmara Havzasi

D02A143 KAZANDERE KÜÇÜKYAYLA

YERİ : **KIRKLARELİ VIZENIN KÖMÜRKÖYDEN KIYIKÖY ISTIKAMETINE 100.METRESINDEN SOLA ORMAN YOLUNDA 800. METRESİNDE SOLDADIR E 19**
27°51'0" Doğu - 41°38'0" Kuzey

YAĞIŞ ALANI : **62,67 km2** **YAKLAŞIK KOT : 174 m**

GÖZLEM SÜRESİ : **01.12.2004 - 30.09.2006**

ORTALAMA AKIMLAR : **Gözlem süresinde 0.970 m3/sn. (1 Yıllık) 2006 Su yılında 0.970 m3/sn.**

ANLIK EN ÇOK VE EN AZ AKIMLAR:

2006 Su yılında anlık ençok akım	**:**	**29.8**	**m3/sn**	**03.07.2006**
2006 Su yılında anlık enaz akım	**:**	**0.021**	**m3/sn**	**01.10.2005**
Gözlem süresinde anlık ençok akım	**:**	**29.8**	**m3/sn**	**03.07.2006**
Gözlem süresinde anlık enaz akım	**:**	**0.021**	**m3/sn**	**01.10.2005**

İstasyon için kullanılmış anahtar bulunamadı.

Akımlar 01 Ekim 2005 'den 30 Eylül 2006' a kadar m3/sn olarak

Gün	Ekim	Kasım	Aralık	Ocak	Şubat	Mart	Nisan	Mayıs	Haziran	Temmuz	Ağustos	Eylül
01	0.021	0.200	0.220	2.05	2.98	7.04	7.04	0.400	0.140	0.140	0.064	0.064
02	0.021	0.200	0.200	1.42	3.08	4.94	4.94	0.350	0.140	0.553	0.064	0.064
03	0.021	0.220	0.260	1.07	3.28	6.15	6.15	0.350	0.140	13.9	0.064	0.064
04	0.021	0.220	0.220	0.955	3.38	4.72	4.72	0.350	0.140	2.19	0.064	0.064
05	0.021	0.220	0.200	0.840	3.38	3.99	3.99	0.350	0.114	1.35	0.064	0.114
06	0.021	0.220	0.200	0.955	2.98	3.48	3.48	0.350	0.200	1.07	0.064	0.114
07	0.021	0.220	0.140	1.07	2.88	4.61	4.61	0.350	0.140	0.420	0.064	0.064
08	0.021	0.220	0.260	0.898	2.78	3.38	3.38	0.350	0.140	0.350	0.064	0.064
09	0.021	0.220	0.553	0.783	2.88	1.55	1.55	0.350	2.88	0.300	0.064	0.064
10	0.021	0.220	0.350	0.668	3.28	1.28	1.42	0.350	0.898	0.260	0.114	0.064
11	0.021	0.220	0.260	0.668	3.99	1.14	1.14	0.350	0.495	0.260	0.114	0.064
12	0.021	0.220	0.300	0.668	3.79	1.01	1.01	0.350	0.350	0.220	0.114	0.064
13	0.021	0.260	0.300	0.553	3.48	0.898	0.610	0.350	0.400	0.220	0.064	0.064
14	0.021	0.260	0.260	0.553	3.28	0.725	0.553	0.300	0.553	0.200	0.064	0.064
15	0.064	0.260	0.260	0.553	3.08	0.725	0.553	0.300	0.420	0.200	0.064	0.064
16	0.114	0.300	0.350	0.553	2.88	0.725	0.495	0.300	0.400	0.200	0.064	0.064
17	0.114	0.300	0.400	0.553	3.58	0.725	0.495	0.260	0.400	0.200	0.064	0.064
18	0.114	0.350	0.783	0.553	10.3	0.725	0.495	0.260	0.350	0.140	0.064	0.064
19	0.114	0.350	0.668	2.05	7.49	0.725	0.495	0.260	0.300	0.140	0.064	0.064
20	0.114	0.400	0.610	1.76	6.26	0.725	0.495	0.260	0.260	0.140	0.064	0.064
21	0.114	0.220	0.495	1.28	4.83	0.725	0.420	0.260	0.260	0.140	0.064	0.064
22	0.114	0.140	0.420	1.21	4.09	0.725	0.420	0.220	0.220	0.140	0.064	0.114
23	0.114	0.114	0.400	1.01	3.58	0.725	0.420	0.220	0.220	0.114	0.114	0.114
24	0.140	0.955	0.400	0.898	3.38	0.725	0.400	0.220	0.220	0.114	0.114	0.220
25	0.140	1.62	0.350	0.898	4.61	0.725	0.400	0.220	0.200	0.114	0.114	0.220
26	0.140	0.898	0.350	0.898	8.85	0.725	0.400	0.220	0.200	0.064	0.114	0.114
27	0.140	0.553	3.18	0.840	8.62	0.725	0.400	0.220	0.200	0.064	0.114	0.064
28	0.140	0.495	6.93	0.783	5.49	0.725	0.400	0.200	0.200	0.064	0.064	0.114
29	0.140	0.350	2.19	0.725	-----	0.725	0.400	0.200	0.140	0.064	0.064	0.200
30	0.140	0.260	1.55	1.48	-----	0.725	0.400	0.200	0.140	0.064	0.042	0.260
31	0.200	-----	6.04	2.68	-----	0.725	-----	0.140	-----	0.064	0.042	-----
Maks.	0.200	1.98	15.3	2.98	14.9	8.73	8.73	0.400	12.0	29.8	0.140	0.260
Min.	0.021	0.114	0.140	0.420	2.68	0.725	0.400	0.140	0.114	0.042	0.021	0.042
Ortalama	0.079	0.356	0.939	1.03	4.37	1.85	1.72	0.286	0.362	0.757	0.075	0.095
LT/SN/Km2	1.26	5.68	15.0	16.4	69.8	29.5	27.5	4.56	5.78	12.1	1.20	1.52
AKIM mm.	3.38	14.7	40.1	43.9	169.	78.9	71.3	12.2	15.0	32.3	3.23	3.95
MİL. M3	0.212	0.923	2.51	2.75	10.6	4.95	4.47	0.766	0.938	2.03	0.202	0.247

SU YILI (2006) YILLIK TOPLAM AKIM 30.60 MİLYON M3 488 MM. 15.5 LT/SN/Km2

03

SUSURLUK HAVZASI

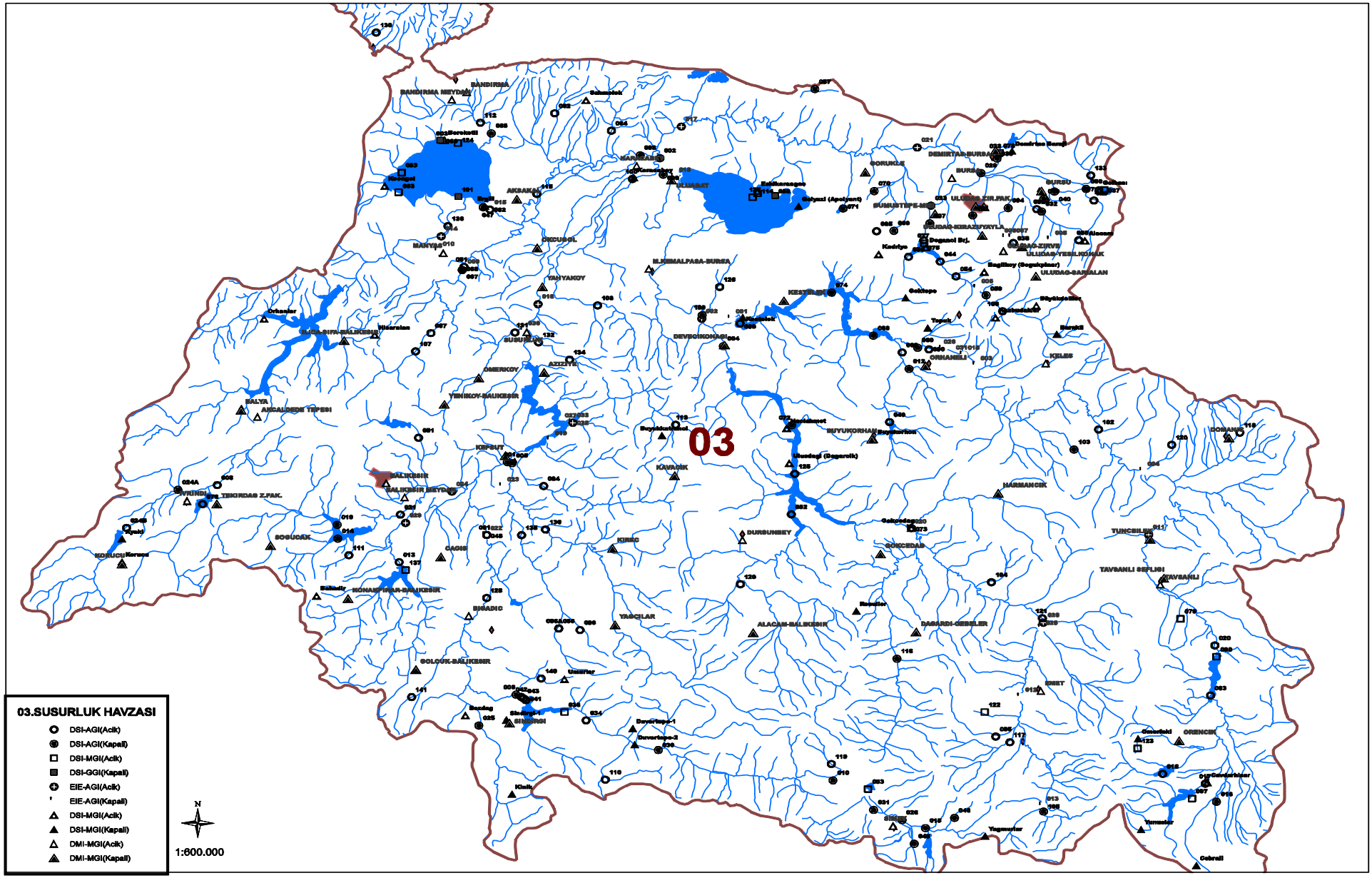
03
03.SUSURLUK HAVZASI
DSI-AGI(Acik)
DSI-AGI(Kapali)
DSI-MGI(Acik)
DSI-GGI(Kapali)
EIE-AGI(Acik)
EIE-AGI(Kapali)
DSI-MGI(Acik)
DSI-MGI(Kapali)
DMI-MGI(Acik)
DMI-MGI(Kapali)
N
1:600.000

03. Susurluk Havzasi

D03A008 MADRA ÇAYI Kahve

YERİ : BALIKESIR-EDREMIT KARAYOLUNUN 30 KM.SINDE.BALYA YOL AYIRIMI UZERINDEKI KOPRUNÜN 50 M MANSABINDADIR.
27°32'44" Doğu - 39°36'53" Kuzey

YAĞIŞ ALANI : 784.45 km2 YAKLAŞIK KOT : 181 m

GÖZLEM SÜRESİ : 01.12.1962 - 30.09.2006

ORTALAMA AKIMLAR : Gözlem süresinde 5.628 m3/sn. (14 Yıllık) 2006 Su yılında 6.425 m3/sn.

ANLIK EN ÇOK VE EN AZ AKIMLAR:

2006 Su yılında anlık ençok akım	:	321.	m3/sn	11.02.2006
2006 Su yılında anlık enaz akım	:	0.048	m3/sn	22.07.2006
Gözlem süresinde anlık ençok akım	:	1400	m3/sn	11.01.1968
Gözlem süresinde anlık enaz akım	:	0.000	m3/sn	04.08.1977

17. Anahtar Eğrisi (Seviyeler cm olarak)

Seviye	Akım	Seviye	Akım	Seviye	Akım	Seviye	Akım
1	0.030	30	6.0	200	147.	430	460.
4	0.094	60	21.7	250	206.	500	565.
7	0.185	90	42.0	320	300.	560	680.
12	0.520	120	66.0	380	382.	580	720.
20	2.2	150	94.0	400	410.	630	824.

Akımlar 01 Ekim 2005 'den 30 Eylül 2006' a kadar m3/sn olarak

Gün	Ekim	Kasım	Aralık	Ocak	Şubat	Mart	Nisan	Mayıs	Haziran	Temmuz	Ağustos	Eylül
01	0.150	0.275	2.52	9.08	7.32	26.1	6.88	3.20	0.680	0.680	0.048	0.185
02	0.220	0.330	2.18	6.44	8.20	17.7	6.44	3.20	0.840	0.680	0.048	0.185
03	1.00	0.425	1.94	5.20	9.08	23.0	6.44	2.86	0.840	0.680	0.048	0.185
04	0.840	0.425	1.69	4.40	9.08	16.3	6.00	2.86	0.680	0.680	0.048	0.185
05	0.520	0.425	1.69	4.00	9.96	14.1	5.60	2.52	0.680	0.520	0.048	0.185
06	0.275	0.425	1.46	4.40	61.5	12.2	5.60	2.52	0.680	0.425	0.048	0.185
07	0.220	0.425	1.46	3.60	22.3	41.3	5.20	2.52	0.680	0.330	0.048	0.150
08	0.185	0.425	1.46	3.60	15.0	83.2	7.76	2.52	0.680	0.275	0.048	0.150
09	0.220	0.520	1.94	3.20	12.7	26.7	7.32	2.52	1.00	0.275	0.048	0.120
10	0.275	0.425	1.46	3.20	113.	19.7	6.00	2.52	1.46	0.220	0.048	0.120
11	0.275	0.520	1.46	4.00	176.	39.9	5.60	2.18	1.23	0.220	0.048	0.150
12	0.220	0.520	1.46	3.60	39.9	52.9	5.20	2.18	1.00	0.220	0.048	0.150
13	0.220	0.520	1.23	3.60	26.1	51.9	4.80	2.18	1.23	0.185	0.048	0.150
14	0.220	0.680	1.23	3.60	19.0	51.0	4.80	2.18	1.46	0.185	0.048	0.120
15	0.275	0.680	1.23	3.20	13.2	32.2	4.80	1.94	1.46	0.185	0.048	0.150
16	0.220	0.680	1.46	2.86	10.9	25.5	4.40	1.94	1.23	0.150	0.048	0.150
17	0.275	0.680	1.69	2.86	10.9	18.4	4.40	1.69	1.23	0.150	0.048	0.120
18	0.275	1.46	14.5	2.52	17.7	23.6	4.40	1.69	1.23	0.120	0.048	0.120
19	0.275	1.46	27.4	15.7	17.7	22.3	4.00	1.69	1.00	0.120	0.048	0.185
20	0.330	2.52	7.76	24.2	17.7	17.0	4.00	1.46	1.00	0.094	0.048	0.185
21	0.330	1.94	5.20	11.8	14.5	14.1	4.00	1.46	1.00	0.094	0.048	0.220
22	0.330	1.23	4.00	9.52	12.7	12.7	3.60	1.46	1.00	0.094	0.048	0.150
23	0.330	1.23	3.20	14.5	11.3	11.8	3.60	1.23	1.00	0.070	0.048	0.150
24	0.330	1.69	2.86	10.4	20.4	13.6	3.20	1.23	0.840	0.070	0.048	0.150
25	0.330	26.1	2.52	9.52	128.	11.8	3.20	1.00	0.840	0.048	0.048	0.220
26	0.330	14.1	2.52	8.64	56.7	10.4	3.20	1.00	0.840	0.048	0.048	0.150
27	0.330	8.20	2.18	7.76	40.6	9.96	3.20	0.840	0.840	0.048	0.070	0.150
28	0.330	6.00	2.52	6.88	37.1	9.08	2.86	0.840	0.840	0.048	0.120	0.150
29	0.330	4.00	6.88	6.44	-----	8.20	2.86	0.840	0.680	0.048	0.120	0.185
30	0.330	3.20	6.88	6.88	-----	7.76	3.20	0.840	0.680	0.048	0.120	0.680
31	0.330	-----	11.8	6.44	-----	7.32	-----	0.680	-----	0.048	0.185	-----
Maks.	1.00	150.	197.	107.	321.	187.	15.7	3.60	1.69	0.680	0.275	9.08
Min.	0.150	0.220	1.23	2.52	7.32	7.32	2.86	0.520	0.520	0.048	0.048	0.094
Ortalama	0.326	2.72	4.12	6.84	33.5	23.6	4.75	1.86	0.962	0.228	0.060	0.178
LT/SN/Km2	0.416	3.46	5.25	8.72	42.7	30.1	6.06	2.38	1.23	0.290	0.077	0.227
AKIM mm.	1.11	8.98	14.1	23.4	103.	80.6	15.7	6.37	3.18	0.777	0.205	0.588
MİL. M3	0.874	7.04	11.0	18.3	81.1	63.2	12.3	4.99	2.49	0.610	0.161	0.461

SU YILI (2006) YILLIK TOPLAM AKIM 202.53 MİLYON M3 258 MM. 8.2 LT/SN/Km2

03. Susurluk Havzasi

D03A013 KİLLE ÇAYI IKİZCETEPELER

YERİ : BALIKESIR-IKIZCETEPELER BARAJININ 1 KM.MANSABINDADIR.
27°55'41" Doğu - 39°30'15" Kuzey

YAĞIŞ ALANI : 470.40 km2 YAKLAŞIK KOT : 123 m

GÖZLEM SÜRESİ : 01.12.1963 - 30.09.2006

ORTALAMA AKIMLAR : Gözlem süresinde 3.357 m3/sn. (33 Yıllık) 2006 Su yılında 0.519 m3/sn.

ANLIK EN ÇOK VE EN AZ AKIMLAR:

2006 Su yılında anlık ençok akım	:	3.30	m3/sn	06.09.2006
2006 Su yılında anlık enaz akım	:	0.200	m3/sn	01.10.2005
Gözlem süresinde anlık ençok akım	:	430.	m3/sn	04.01.1987
Gözlem süresinde anlık enaz akım	:	0.000	m3/sn	28.06.1985

14. Anahtar Eğrisi (Seviyeler cm olarak)

Seviye	Akım	Seviye	Akım	Seviye	Akım	Seviye	Akım
9	0.008	56	10.0	168	125.	268	270.
18	0.160	70	18.0	183	145.	297	310.
27	0.900	99	43.0	201	165.	317	350.
36	2.6	131	77.0	215	190.	343	390.
46	5.5	151	100.	237	220.	370	430.

Akımlar 01 Ekim 2005 'den 30 Eylül 2006' a kadar m3/sn olarak

Gün	Ekim	Kasım	Aralık	Ocak	Şubat	Mart	Nisan	Mayıs	Haziran	Temmuz	Ağustos	Eylül
01	0.200	0.250	0.330	0.250	0.250	0.200	0.410	0.490	0.330	0.410	0.410	1.70
02	0.200	0.250	0.250	0.250	0.330	0.200	0.410	0.490	0.330	0.410	0.410	2.10
03	0.200	0.250	0.200	0.250	0.330	0.330	0.410	0.490	0.330	0.410	0.490	1.95
04	0.200	0.250	0.200	0.250	0.330	0.330	0.410	0.490	0.330	0.410	0.490	1.95
05	0.200	0.200	0.200	0.250	0.330	0.330	0.410	0.410	0.330	0.410	0.490	2.30
06	0.200	0.200	0.200	0.250	0.690	0.330	0.490	0.410	0.330	0.410	0.490	2.60
07	0.200	0.200	0.200	0.250	0.330	0.330	0.410	0.490	0.330	0.490	0.490	2.60
08	0.200	0.200	0.200	0.250	0.250	0.690	0.490	0.490	0.330	0.490	0.490	2.60
09	0.200	0.200	0.200	0.250	0.330	0.490	0.490	0.490	0.410	0.490	0.490	2.60
10	0.200	0.200	0.200	0.250	0.580	0.410	0.490	0.580	0.330	0.490	0.490	2.60
11	0.200	0.200	0.200	0.250	0.690	0.580	0.490	0.580	0.330	0.490	0.490	2.60
12	0.200	0.200	0.200	0.250	0.410	0.580	0.490	0.580	0.330	0.410	0.490	2.30
13	0.200	0.200	0.200	0.250	0.330	0.410	0.580	0.580	0.330	0.410	0.490	2.60
14	0.200	0.200	0.200	0.250	0.330	0.580	0.490	0.490	0.330	0.410	0.490	2.60
15	0.200	0.200	0.200	0.250	0.330	0.490	0.490	0.490	0.330	0.410	0.490	2.60
16	0.200	0.200	0.200	0.250	0.330	0.410	0.490	0.490	0.410	0.410	0.410	2.60
17	0.200	0.200	0.200	0.250	0.330	0.410	0.490	0.580	0.330	0.410	0.410	2.30
18	0.200	0.250	0.200	0.250	0.250	0.490	0.490	0.490	0.410	0.410	0.410	2.30
19	0.200	0.250	0.250	0.330	0.250	0.410	0.490	0.490	0.410	0.490	0.410	2.60
20	0.200	0.250	0.250	0.330	0.250	0.410	0.490	0.490	0.410	0.410	0.410	2.60
21	0.200	0.250	0.250	0.330	0.200	0.410	0.490	0.410	0.410	0.490	0.410	2.60
22	0.200	0.250	0.250	0.330	0.200	0.410	0.490	0.410	0.410	0.580	0.410	2.60
23	0.200	0.250	0.250	0.410	0.200	0.410	0.490	0.330	0.410	0.580	0.410	2.60
24	0.200	0.250	0.250	0.330	0.200	0.410	0.490	0.330	0.410	0.580	0.410	2.60
25	0.200	0.250	0.250	0.330	0.200	0.410	0.490	0.330	0.410	0.690	0.410	2.30
26	0.200	0.330	0.250	0.330	0.200	0.410	0.490	0.330	0.490	0.690	0.490	1.95
27	0.200	0.330	0.250	0.330	0.200	0.410	0.490	0.330	0.410	0.410	0.410	1.95
28	0.200	0.330	0.250	0.250	0.200	0.410	0.490	0.330	0.410	0.410	0.410	1.95
29	0.200	0.330	0.250	0.330	-----	0.410	0.490	0.330	0.410	0.410	0.410	1.95
30	0.200	0.330	0.250	0.330	-----	0.410	0.490	0.330	0.410	0.410	0.410	1.95
31	0.250	-----	0.250	0.330	-----	0.410	-----	0.330	-----	0.410	0.790	-----
Maks.	0.250	0.330	0.330	0.410	0.690	0.690	0.690	0.690	0.580	0.690	0.790	3.30
Min.	0.200	0.200	0.200	0.250	0.200	0.200	0.410	0.330	0.330	0.410	0.410	1.70
Ortalama	0.202	0.242	0.227	0.284	0.316	0.417	0.477	0.448	0.373	0.463	0.458	2.35
LT/SN/Km2	0.429	0.514	0.482	0.603	0.672	0.886	1.01	0.952	0.792	0.983	0.974	5.00
AKIM mm.	1.15	1.33	1.29	1.61	1.63	2.37	2.63	2.55	2.05	2.63	2.61	13.0
MİL. M3	0.540	0.626	0.607	0.759	0.765	1.12	1.24	1.20	0.966	1.24	1.23	6.10

SU YILI (2006) YILLIK TOPLAM AKIM 16.39 MİLYON M3 35 MM. 1.1 LT/SN/Km2

03. Susurluk Havzasi

D03A018 KIZIK S. AĞARİ

YERİ : KÜTAHYA-ÇAVDARHİSAR AĞARİ KÖYÜ İÇERESİNDEDİR
29°33'32" Doğu - 39°13'16" Kuzey

YAĞIŞ ALANI : 60.90 km2 YAKLAŞIK KOT : 1039 m

GÖZLEM SÜRESİ : 01.10.1966 - 30.09.2006

ORTALAMA AKIMLAR : Gözlem süresinde 3.062 m3/sn. (36 Yıllık) 2006 Su yılında 0.251 m3/sn.

ANLIK EN ÇOK VE EN AZ AKIMLAR:

2006 Su yılında anlık ençok akım	:	7.80	m3/sn	03.03.2006
2006 Su yılında anlık enaz akım	:	0.004	m3/sn	02.08.2006
Gözlem süresinde anlık ençok akım	:	80.0	m3/sn	01.11.1974
Gözlem süresinde anlık enaz akım	:	0.000	m3/sn	20.07.1967

Akımlar 01 Ekim 2005 'den 30 Eylül 2006' a kadar m3/sn olarak

Gün	Ekim	Kasım	Aralık	Ocak	Şubat	Mart	Nisan	Mayıs	Haziran	Temmuz	Ağustos	Eylül
01	0.068	0.048	0.068	0.094	0.094	1.40	0.420	0.250	0.160	0.094	0.068	0.048
02	0.068	0.048	0.068	0.094	0.094	1.30	0.420	0.250	0.160	0.094	0.048	0.048
03	0.068	0.048	0.068	0.094	0.068	3.10	0.420	0.250	0.160	0.094	0.048	0.048
04	0.068	0.048	0.068	0.094	0.094	1.70	0.420	0.250	0.160	0.094	0.068	0.048
05	0.068	0.048	0.068	0.094	0.094	1.20	0.420	0.250	0.160	0.094	0.068	0.048
06	0.068	0.048	0.068	0.094	0.094	0.940	0.420	0.250	0.160	0.094	0.068	0.048
07	0.048	0.048	0.068	0.094	0.094	1.05	0.420	0.350	0.160	0.094	0.068	0.048
08	0.048	0.048	0.068	0.094	0.094	1.30	0.350	0.420	0.160	0.120	0.068	0.048
09	0.048	0.048	0.068	0.094	0.094	1.05	0.350	0.350	0.160	0.120	0.068	0.048
10	0.048	0.048	0.068	0.094	0.200	0.940	0.350	0.350	0.160	0.094	0.068	0.048
11	0.048	0.048	0.068	0.094	3.00	0.940	0.350	0.350	0.160	0.094	0.068	0.048
12	0.048	0.048	0.068	0.094	1.55	0.940	0.300	0.350	0.160	0.068	0.068	0.048
13	0.048	0.048	0.068	0.094	0.940	0.940	0.300	0.350	0.160	0.068	0.068	0.048
14	0.048	0.048	0.068	0.094	0.840	1.30	0.350	0.350	0.160	0.068	0.068	0.048
15	0.048	0.048	0.068	0.094	0.660	1.05	0.350	0.350	0.160	0.068	0.068	0.048
16	0.048	0.048	0.068	0.094	0.500	1.05	0.350	0.300	0.160	0.068	0.048	0.048
17	0.048	0.048	0.068	0.094	0.420	1.05	0.300	0.250	0.160	0.068	0.048	0.048
18	0.048	0.048	0.068	0.094	0.660	1.05	0.300	0.300	0.160	0.068	0.048	0.048
19	0.048	0.048	0.250	0.120	1.20	1.05	0.300	0.300	0.160	0.068	0.048	0.048
20	0.048	0.048	0.094	0.120	1.30	1.05	0.300	0.300	0.160	0.068	0.048	0.048
21	0.048	0.048	0.094	0.120	1.40	0.740	0.300	0.300	0.160	0.068	0.048	0.048
22	0.048	0.048	0.094	0.120	1.40	0.560	0.300	0.300	0.160	0.068	0.048	0.048
23	0.048	0.048	0.094	0.120	1.30	0.560	0.300	0.300	0.094	0.068	0.048	0.048
24	0.048	0.068	0.068	0.094	1.30	0.560	0.250	0.200	0.094	0.068	0.048	0.048
25	0.048	0.068	0.068	0.094	2.10	0.560	0.250	0.160	0.094	0.068	0.048	0.048
26	0.048	0.068	0.068	0.094	2.00	0.560	0.250	0.160	0.094	0.068	0.048	0.048
27	0.048	0.068	0.068	0.094	1.70	0.560	0.250	0.160	0.094	0.068	0.048	0.048
28	0.048	0.068	0.068	0.094	1.40	0.500	0.250	0.160	0.094	0.068	0.048	0.048
29	0.048	0.068	0.068	0.094	-----	0.500	0.250	0.160	0.094	0.068	0.048	0.048
30	0.048	0.068	0.068	0.094	-----	0.420	0.250	0.160	0.094	0.068	0.048	0.048
31	0.048	-----	0.068	0.094	-----	0.420	-----	0.160	-----	0.068	0.048	-----
Maks.	0.068	0.068	1.70	0.660	4.80	7.80	0.420	0.840	0.500	0.160	0.200	0.048
Min.	0.048	0.048	0.048	0.094	0.048	0.420	0.250	0.094	0.048	0.032	0.004	0.048
Ortalama	0.052	0.053	0.077	0.098	0.882	0.979	0.328	0.271	0.142	0.079	0.056	0.048
LT/SN/Km2	0.852	0.865	1.27	1.61	14.5	16.1	5.39	4.44	2.34	1.30	0.926	0.788
AKIM mm.	2.28	2.24	3.40	4.32	35.0	43.0	14.0	11.9	6.06	3.47	2.48	2.04
MİL. M3	0.139	0.137	0.207	0.263	2.13	2.62	0.850	0.725	0.369	0.211	0.151	0.124

SU YILI (2006) YILLIK TOPLAM AKIM 7.93 MİLYON M3 130 MM. 4.1 LT/SN/Km2

03. Susurluk Havzasi

D03A021 ÜZÜMCÜ ÇAYI KÜÇÜK BOSTANCI

YERİ : BALIKESIR-BIGADIC KARAYOLUNUN 8.KM SINDEKI KOPRUNUN 100 M.MENBAI`NDADIR
27°55'33" Doğu - 39°35'4" Kuzey

YAĞIŞ ALANI : 521.50 km2 YAKLAŞIK KOT : 100 m

GÖZLEM SÜRESİ : 01.07.1964 - 30.09.2006

ORTALAMA AKIMLAR : Gözlem süresinde 2.639 m3/sn. (31 Yıllık) 2006 Su yılında 2.639 m3/sn.

ANLIK EN ÇOK VE EN AZ AKIMLAR:

2006 Su yılında anlık ençok akım	:	283.	m3/sn	11.03.2006
2006 Su yılında anlık enaz akım	:	0.000	m3/sn	26.07.2006
Gözlem süresinde anlık ençok akım	:	990.	m3/sn	11.01.1968
Gözlem süresinde anlık enaz akım	:	0.000	m3/sn	11.08.1972

10. Anahtar Eğrisi (Seviyeler cm olarak)

Seviye	Akım	Seviye	Akım	Seviye	Akım	Seviye	Akım
1	0.000	91	25.0	191	63.0	280	200.
20	2.3	122	32.0	207	74.0	298	250.
37	8.4	143	39.0	223	92.0	317	330.
53	13.5	159	45.0	244	120.	333	420.
69	19.0	175	53.0	264	160.	349	520.

Akımlar 01 Ekim 2005 'den 30 Eylül 2006' a kadar m3/sn olarak

Gün	Ekim	Kasım	Aralık	Ocak	Şubat	Mart	Nisan	Mayıs	Haziran	Temmuz	Ağustos	Eylül
01	0.020	0.105	1.10	4.40	2.90	11.0	2.90	1.30	0.560	0.160	0.105	0.235
02	0.020	0.105	0.940	2.60	3.30	7.40	2.60	1.30	0.560	0.160	0.105	0.160
03	0.020	0.105	0.940	1.75	3.60	7.40	2.30	1.30	0.440	0.160	0.105	0.105
04	0.020	0.105	0.800	1.30	4.40	6.60	2.30	1.10	0.560	0.160	0.160	0.105
05	0.020	0.105	0.800	1.10	5.50	5.50	2.30	1.10	0.440	0.105	0.105	0.105
06	0.050	0.105	0.800	1.10	21.0	4.40	2.00	1.10	0.440	0.105	0.105	0.050
07	0.105	0.105	0.680	1.10	12.5	6.20	2.00	1.10	0.440	0.105	0.105	0.105
08	0.235	0.105	0.680	1.10	8.70	34.0	2.00	1.10	0.440	0.105	0.105	0.160
09	0.160	0.105	1.30	0.940	7.00	12.5	2.30	1.10	0.440	0.105	0.105	0.160
10	0.105	0.105	0.940	0.940	21.0	9.50	2.00	1.10	0.560	0.105	0.160	0.160
11	0.105	0.105	0.800	0.940	76.0	17.0	2.00	1.50	0.800	0.105	0.105	0.160
12	0.105	0.160	0.680	0.940	18.5	39.0	1.75	1.10	0.800	0.105	0.105	0.160
13	0.105	0.160	0.680	1.10	10.0	13.5	1.75	1.50	0.800	0.105	0.105	0.160
14	0.105	0.105	0.680	0.940	7.40	28.0	1.75	1.30	1.10	0.105	0.105	0.235
15	0.050	0.105	0.680	0.800	5.80	14.5	1.75	1.10	0.940	0.105	0.105	0.340
16	0.105	0.105	0.680	0.800	4.60	11.0	1.50	0.940	0.800	0.105	0.105	0.340
17	0.105	0.160	0.680	0.800	4.00	9.10	1.50	0.940	0.680	0.050	0.235	0.235
18	0.105	0.235	0.680	0.800	7.60	9.50	1.50	0.940	0.680	0.050	0.105	0.105
19	0.160	0.235	8.00	3.30	11.5	13.5	1.50	0.800	0.560	0.105	0.235	0.105
20	0.160	0.560	4.40	12.5	8.00	8.70	1.50	0.800	0.440	0.160	0.050	0.050
21	0.105	0.680	2.60	6.20	6.20	7.60	1.50	0.680	0.340	0.235	0.440	0.050
22	0.105	0.560	1.75	4.40	4.60	6.60	1.50	0.680	0.340	0.235	0.235	0.560
23	0.105	0.440	1.50	9.10	4.00	5.80	1.30	0.680	0.340	0.235	0.235	0.680
24	0.105	0.440	1.30	6.20	3.60	5.50	1.30	0.680	0.235	0.160	0.340	2.90
25	0.160	0.680	1.10	4.60	20.0	5.80	1.30	0.680	0.235	0.050	0.235	2.30
26	0.105	10.0	0.940	4.40	15.5	5.50	1.30	0.680	0.235	0.050	0.160	0.940
27	0.105	7.40	0.940	4.40	20.0	5.10	1.30	0.680	0.235	0.050	0.105	0.235
28	0.105	4.40	0.800	4.00	15.5	4.40	1.30	0.680	0.160	0.160	0.160	1.10
29	0.105	2.00	0.800	3.60	-----	3.60	1.30	0.680	0.160	0.105	0.235	7.40
30	0.105	1.30	4.60	3.30	-----	2.90	1.30	0.680	0.160	0.105	0.160	8.00
31	0.105	-----	3.30	2.90	-----	2.90	-----	0.560	-----	0.105	0.235	-----
Maks.	0.340	21.0	16.5	25.0	175.	283.	2.90	2.00	1.30	0.235	0.440	10.5
Min.	0.020	0.105	0.560	0.680	2.90	2.90	1.30	0.560	0.160	KURU	0.020	0.020
Ortalama	0.099	1.03	1.50	2.98	11.9	10.5	1.75	0.964	0.497	0.121	0.160	0.913
LT/SN/Km2	0.190	1.97	2.88	5.71	22.8	20.0	3.36	1.85	0.954	0.232	0.306	1.75
AKIM mm.	0.509	5.12	7.72	15.3	55.1	53.7	8.71	4.95	2.47	0.622	0.821	4.54
MİL. M3	0.265	2.67	4.02	7.98	28.7	28.0	4.54	2.58	1.29	0.324	0.428	2.37

SU YILI (2006) YILLIK TOPLAM AKIM 83.17 MİLYON M3 159 MM. 5.1 LT/SN/Km2

03. Susurluk Havzasi

D03A024 MADRA ÇAYI Ayakli

YERİ : İVRINDI-AYAKLI KOYUNÜN 1.5 KM KUZEYİNDEDİR.
27°22'7" Doğu - 39°31'46" Kuzey

YAĞIŞ ALANI : 239.30 km2 YAKLAŞIK KOT : 250 m

GÖZLEM SÜRESİ : 01.10.1966 - 30.09.2006

ORTALAMA AKIMLAR : Gözlem süresinde 2.704 m3/sn. (40 Yıllık) 2006 Su yılında 3.251 m3/sn.

ANLIK EN ÇOK VE EN AZ AKIMLAR:

2006 Su yılında anlık ençok akım	:	75.5	m3/sn	11.02.2006
2006 Su yılında anlık enaz akım	:	0.000	m3/sn	07.09.2006
Gözlem süresinde anlık ençok akım	:	800.	m3/sn	11.01.1968
Gözlem süresinde anlık enaz akım	:	0.000	m3/sn	07.09.2006

15. Anahtar Eğrisi (Seviyeler cm olarak)

Seviye	Akım	Seviye	Akım	Seviye	Akım	Seviye	Akım
13	0.008	42	3.7	89	21.0	150	53.0
18	0.078	56	8.0	94	24.0	210	93.0
23	0.320	74	15.0	99	26.0	260	140.
28	0.820	79	17.0	104	29.0	310	200.
34	1.8	84	19.0	109	31.0	400	370.

Akımlar 01 Ekim 2005 'den 30 Eylül 2006' a kadar m3/sn olarak

Gün	Ekim	Kasım	Aralık	Ocak	Şubat	Mart	Nisan	Mayıs	Haziran	Temmuz	Ağustos	Eylül
01	0.405	0.223	1.29	6.45	4.50	14.9	5.00	2.30	0.560	0.223	0.048	0.013
02	0.405	0.223	1.29	4.75	4.75	12.1	4.75	2.10	0.660	0.223	0.048	0.013
03	0.405	0.223	1.14	4.00	4.50	16.7	4.25	2.10	0.560	0.405	0.048	0.005
04	0.405	0.172	1.14	3.50	4.75	12.9	4.25	1.92	0.560	0.330	0.048	0.005
05	0.330	0.172	1.00	3.00	5.29	11.0	4.25	1.92	0.560	0.330	0.021	0.013
06	0.330	0.172	0.860	3.00	16.7	9.26	4.00	1.92	0.480	0.275	0.021	KURU
07	0.330	0.172	0.760	2.50	10.6	18.6	3.75	1.75	0.480	0.275	0.021	KURU
08	0.330	0.172	0.760	2.30	7.90	27.0	5.00	1.92	0.560	0.275	0.013	KURU
09	0.330	0.172	0.760	2.10	6.74	16.2	4.50	1.92	0.860	0.223	0.003	KURU
10	0.330	0.172	0.760	2.10	33.5	12.9	4.25	1.75	1.00	0.223	0.010	KURU
11	0.275	0.172	0.760	1.92	41.6	15.8	4.00	1.75	0.860	0.172	0.010	KURU
12	0.275	0.172	0.760	1.92	18.6	26.0	3.50	1.75	0.760	0.172	0.013	KURU
13	0.275	0.172	0.760	1.75	12.1	25.0	3.75	1.75	0.760	0.172	0.013	KURU
14	0.275	0.172	0.760	1.75	9.60	26.0	3.50	1.57	0.760	0.172	0.010	KURU
15	0.275	0.172	0.760	1.75	7.90	19.1	3.50	1.57	0.660	0.120	0.005	KURU
16	0.275	0.172	0.860	1.57	6.74	15.3	3.00	1.43	0.560	0.120	0.005	KURU
17	0.275	0.172	1.14	1.43	6.45	12.9	2.75	1.43	0.560	0.120	0.005	KURU
18	0.223	0.275	9.60	1.29	8.58	13.3	2.75	1.29	0.480	0.092	0.010	KURU
19	0.223	0.330	10.6	10.6	9.60	11.7	2.75	1.29	0.405	0.092	0.010	KURU
20	0.223	0.405	4.75	14.1	9.94	10.3	2.75	1.29	0.405	0.120	0.013	KURU
21	0.223	0.405	3.50	7.90	9.26	9.60	2.75	1.29	0.330	0.120	0.010	KURU
22	0.223	0.330	2.75	6.45	8.24	8.58	2.50	1.14	0.275	0.092	0.005	0.001
23	0.223	0.330	2.30	7.03	7.61	7.90	2.30	1.14	0.275	0.092	0.005	0.001
24	0.223	0.275	1.92	6.16	9.60	8.24	2.30	1.00	0.275	0.120	0.005	0.003
25	0.223	5.00	1.75	5.58	43.3	7.32	2.30	1.00	0.223	0.120	0.005	0.063
26	0.223	3.25	1.75	5.00	27.5	6.74	2.10	0.860	0.223	0.120	0.005	0.013
27	0.223	3.25	1.57	4.50	23.0	6.45	2.10	0.860	0.223	0.120	0.005	0.092
28	0.223	2.30	1.92	4.00	17.7	5.87	2.10	0.860	0.223	0.120	0.005	0.405
29	0.223	1.75	6.16	4.00	-----	5.58	2.10	0.860	0.223	0.063	0.005	0.760
30	0.223	1.29	4.75	4.00	-----	5.29	2.30	0.660	0.223	0.063	0.005	0.405
31	0.223	-----	9.60	4.00	-----	5.00	-----	0.660	-----	0.063	0.005	-----
Maks.	0.405	5.00	54.5	45.5	75.5	52.5	11.0	3.00	1.29	0.480	0.092	1.75
Min.	0.223	0.172	0.560	1.14	4.50	5.00	2.10	0.560	0.172	0.021	0.003	KURU
Ortalama	0.279	0.742	2.53	4.21	13.4	13.0	3.30	1.45	0.499	0.169	0.014	0.060
LT/SN/Km2	1.17	3.10	10.6	17.6	56.2	54.4	13.8	6.07	2.09	0.705	0.059	0.250
AKIM mm.	3.12	8.04	28.3	47.1	136.	146.	35.8	16.3	5.41	1.89	0.157	0.647
MİL. M3	0.747	1.92	6.78	11.3	32.5	34.9	8.56	3.89	1.29	0.452	0.038	0.155

SU YILI (2006) YILLIK TOPLAM AKIM 102.53 MİLYON M3 428 MM. 13.6 LT/SN/Km2

03. Susurluk Havzasi

D03A025 CÜNEYT ÇAYI CÜNEYT KÖPRÜSÜ

YERİ : SINDIRGI-AKHİSAR KARAYOLUNUN 5.KM DEKI KÖPRÜNÜN 100 M MEMBAINDADIR.
28°7'24" Doğu - 39°13'23" Kuzey

YAĞIŞ ALANI : 194.80 km2 YAKLAŞIK KOT : 225 m

GÖZLEM SÜRESİ : 01.10.2001 - 30.09.2006

ORTALAMA AKIMLAR : Gözlem süresinde 1.884 m3/sn. (4 Yıllık) 2006 Su yılında 1.968 m3/sn.

ANLIK EN ÇOK VE EN AZ AKIMLAR:

2006 Su yılında anlık ençok akım	:	79.0	m3/sn	12.03.2006
2006 Su yılında anlık enaz akım	:	0.000	m3/sn	01.10.2005
Gözlem süresinde anlık ençok akım	:	180.	m3/sn	12.03.1968
Gözlem süresinde anlık enaz akım	:	0.000	m3/sn	01.09.2002

4. Anahtar Eğrisi (Seviyeler cm olarak)

Seviye	Akım	Seviye	Akım	Seviye	Akım	Seviye	Akım
3	0.017	40	3.3	120	24.2	220	65.0
6	0.069	50	5.0	140	31.9	230	69.7
10	0.195	70	9.2	160	40.1	250	79.0
13	0.350	80	11.9	180	48.3	280	94.0
20	0.850	100	17.6	200	56.5	300	104.

Akımlar 01 Ekim 2005 'den 30 Eylül 2006' a kadar m3/sn olarak

Gün	Ekim	Kasım	Aralık	Ocak	Şubat	Mart	Nisan	Mayıs	Haziran	Temmuz	Ağustos	Eylül
01	KURU	0.068	0.762	4.94	3.37	6.16	2.10	1.04	0.290	0.160	0.060	KURU
02	0.036	0.068	0.681	3.22	2.79	4.94	1.93	1.04	0.290	0.160	0.025	KURU
03	0.068	0.068	0.600	2.51	3.08	10.8	1.93	1.04	0.225	0.160	0.025	KURU
04	0.068	0.068	0.522	2.13	3.98	6.16	1.93	1.04	0.225	0.108	0.025	KURU
05	0.068	0.106	0.522	1.90	4.62	4.78	2.10	1.04	0.225	0.108	0.025	KURU
06	0.068	0.106	0.458	2.23	20.0	3.83	1.93	1.04	0.225	0.108	0.025	KURU
07	0.068	0.106	0.458	1.90	10.4	5.10	1.75	1.04	0.225	0.108	0.025	KURU
08	0.068	0.106	0.458	1.75	7.50	9.92	1.75	1.04	0.225	0.108	0.025	KURU
09	0.068	0.106	0.762	1.46	6.16	5.96	1.75	1.04	0.225	0.060	0.025	KURU
10	0.068	0.106	0.681	1.23	14.9	7.44	1.75	1.04	0.225	0.060	0.025	KURU
11	0.068	0.106	0.600	1.13	30.3	10.7	1.75	0.920	0.225	0.060	0.025	KURU
12	0.068	0.106	0.600	1.04	12.4	26.8	1.63	0.920	0.225	0.108	0.025	KURU
13	0.068	0.106	0.522	0.946	8.16	12.2	1.51	0.920	0.225	0.108	0.025	KURU
14	0.036	0.106	0.458	0.946	6.16	16.4	1.51	0.818	0.290	0.060	0.025	KURU
15	0.036	0.106	0.458	0.853	4.94	11.0	1.51	0.818	0.225	0.060	0.025	KURU
16	0.036	0.106	1.32	0.853	3.98	8.76	1.28	0.818	0.225	0.060	KURU	KURU
17	0.036	0.106	3.37	0.853	3.98	7.22	1.16	0.818	0.225	0.060	KURU	KURU
18	0.036	0.853	2.42	0.762	9.92	7.00	1.16	0.717	0.225	0.060	KURU	KURU
19	0.036	0.387	11.0	9.26	10.1	6.20	1.04	0.717	0.160	0.060	KURU	KURU
20	0.036	1.32	4.62	10.1	9.70	5.00	1.04	0.615	0.160	0.060	KURU	KURU
21	0.036	0.681	3.83	5.42	8.16	4.53	1.04	0.534	0.160	0.060	KURU	0.290
22	0.036	0.458	3.52	4.46	7.12	4.05	1.04	0.453	0.160	0.060	KURU	0.060
23	0.036	0.387	3.22	5.58	5.96	3.43	1.16	0.453	0.160	0.060	KURU	0.060
24	0.036	0.458	2.79	3.98	5.58	3.84	1.16	0.453	0.160	0.060	KURU	0.060
25	0.036	1.75	1.13	3.37	11.9	3.43	1.04	0.453	0.160	0.060	KURU	0.060
26	0.036	9.04	1.04	3.37	11.5	2.96	0.920	0.371	0.160	0.060	KURU	0.060
27	0.036	5.58	1.90	3.37	8.60	2.84	0.920	0.371	0.160	0.060	KURU	0.060
28	0.036	2.42	2.51	3.37	6.35	2.58	0.818	0.371	0.160	0.060	KURU	0.160
29	0.036	1.32	3.22	3.37	-----	2.45	0.920	0.371	0.160	0.060	KURU	3.22
30	0.068	0.853	2.65	3.37	-----	2.84	1.04	0.290	0.160	0.060	KURU	0.453
31	0.068	-----	6.92	3.37	-----	2.84	-----	0.290	-----	0.060	KURU	-----
Maks.	0.068	20.0	22.0	40.9	51.2	79.0	2.28	1.04	0.290	0.160	0.060	11.5
Min.	KURU	0.068	0.458	0.681	2.51	2.10	0.818	0.290	0.108	0.060	KURU	KURU
Ortalama	0.048	0.905	2.06	3.00	8.63	6.84	1.42	0.738	0.206	0.081	0.013	0.149
LT/SN/Km2	0.248	4.65	10.6	15.4	44.3	35.1	7.28	3.79	1.05	0.413	0.068	0.767
AKIM mm.	0.664	12.0	28.4	41.3	107.	94.1	18.9	10.2	2.73	1.11	0.182	1.99
MİL. M3	0.129	2.35	5.53	8.04	20.9	18.3	3.68	1.98	0.533	0.216	0.035	0.387

SU YILI (2006) YILLIK TOPLAM AKIM 62.08 MİLYON M3 319 MM. 10.1 LT/SN/Km2

03. Susurluk Havzasi

D03A034 SİMAV ÇAYI OSMANLAR

YERİ : SINDIRGI-SIMAV KARAYOLUNUN 15.KM.SINDEKI OSMANLAR KOYU KOPRUSUNUN 1,5 KM.MANSABINDADIR

28°19'28" Doğu - 39°15'31" Kuzey

YAĞIŞ ALANI : 1253.90 km2 YAKLAŞIK KOT : 271 m

GÖZLEM SÜRESİ : 22.10.1971 - 30.09.2006

ORTALAMA AKIMLAR : Gözlem süresinde 7.431 m3/sn. (34 Yıllık) 2006 Su yılında 11.443 m3/sn.

ANLIK EN ÇOK VE EN AZ AKIMLAR:

2006 Su yılında anlık ençok akım	:	238.	m3/sn	12.03.2006
2006 Su yılında anlık enaz akım	:	0.021	m3/sn	17.08.2006
Gözlem süresinde anlık ençok akım	:	430.	m3/sn	25.12.2001
Gözlem süresinde anlık enaz akım	:	0.000	m3/sn	08.11.1971

18. Anahtar Eğrisi (Seviyeler cm olarak)

Seviye	Akım	Seviye	Akım	Seviye	Akım	Seviye	Akım
1	0.018	154	57.0	184	84.0	231	130.
7	0.239	160	62.0	190	90.0	242	145.
22	1.5	166	67.0	196	96.0	254	160.
66	10.5	172	72.0	202	100.	267	175.
119	35.3	178	78.0	217	115.	310	227.

Akımlar 01 Ekim 2005 'den 30 Eylül 2006' a kadar m3/sn olarak

Gün	Ekim	Kasım	Aralık	Ocak	Şubat	Mart	Nisan	Mayıs	Haziran	Temmuz	Ağustos	Eylül
01	0.145	0.590	1.88	12.8	10.0	52.4	27.4	10.0	1.23	0.480	0.145	0.021
02	0.145	0.590	1.69	10.5	10.5	45.4	25.6	8.25	1.10	0.480	0.145	0.021
03	0.198	0.590	1.50	8.25	10.9	70.8	25.0	6.15	1.10	0.480	0.145	0.032
04	0.327	0.590	1.37	6.50	10.9	58.8	24.4	5.45	0.967	0.480	0.115	0.032
05	0.327	0.590	1.37	5.80	11.4	52.4	23.8	5.80	0.967	0.480	0.115	0.032
06	0.403	0.590	1.37	10.5	55.9	47.5	23.2	5.80	0.967	0.403	0.084	0.032
07	0.403	0.590	1.37	9.56	42.6	44.0	23.2	5.80	0.967	0.403	0.084	0.032
08	0.403	0.590	1.50	8.25	32.8	68.4	23.2	6.50	0.967	0.403	0.054	0.032
09	0.403	0.590	1.69	6.94	28.0	55.9	22.0	6.94	0.833	0.403	0.043	0.032
10	0.403	0.590	1.88	5.80	54.5	49.6	22.0	6.50	0.833	0.403	0.043	0.032
11	0.403	0.700	1.69	5.10	158.	51.0	20.8	5.80	0.833	0.403	0.043	0.043
12	0.403	0.700	1.69	4.40	85.2	162.	19.6	5.45	0.833	0.403	0.043	0.054
13	0.403	0.700	1.50	4.13	62.0	92.6	19.0	5.45	0.833	0.403	0.032	0.084
14	0.403	0.700	1.37	3.86	54.5	98.5	19.6	4.75	0.833	0.403	0.032	0.084
15	0.403	0.700	1.37	3.59	45.4	83.6	19.6	4.40	0.833	0.327	0.032	0.115
16	0.403	0.700	1.50	3.33	38.4	75.6	18.0	4.40	0.833	0.327	0.032	0.115
17	0.480	0.700	3.06	3.06	34.6	66.0	17.5	4.13	0.833	0.327	0.032	0.115
18	0.590	1.69	4.75	2.79	35.8	59.6	16.4	3.86	0.700	0.327	0.032	0.145
19	0.590	1.10	43.3	15.4	37.7	53.1	15.4	3.59	0.590	0.250	0.032	0.115
20	0.590	1.69	15.9	37.0	39.8	46.8	14.4	3.33	0.590	0.250	0.021	0.084
21	0.590	1.69	10.5	20.2	39.1	42.6	13.4	3.06	0.590	0.250	0.021	0.115
22	0.590	1.23	7.38	16.4	37.0	38.4	12.8	2.79	0.590	0.250	0.021	0.198
23	0.590	0.967	5.45	22.0	35.8	35.8	13.9	2.52	0.590	0.250	0.021	0.327
24	0.590	0.967	4.40	18.0	34.6	35.2	12.8	2.25	0.590	0.198	0.021	0.327
25	0.480	1.37	3.59	15.4	46.8	34.6	11.8	2.06	0.590	0.198	0.021	0.403
26	0.590	14.9	3.33	13.9	55.2	32.8	10.9	1.88	0.590	0.198	0.021	0.403
27	0.590	6.15	3.06	12.3	55.2	31.6	10.5	1.69	0.590	0.198	0.021	0.327
28	0.590	3.59	3.33	10.9	51.0	29.8	10.0	1.69	0.480	0.198	0.021	0.403
29	0.590	3.59	4.13	10.0	-----	28.6	10.0	1.50	0.480	0.198	0.021	3.50
30	0.590	2.25	4.40	9.56	-----	28.6	10.0	1.50	0.480	0.198	0.021	2.23
31	0.590	-----	13.4	10.0	-----	28.6	-----	1.37	-----	0.145	0.021	-----
Maks.	0.590	32.8	82.8	86.8	211.	238.	27.4	10.0	1.37	0.480	0.145	7.05
Min.	0.145	0.403	1.10	2.79	9.13	27.4	10.0	0.967	0.403	0.084	0.021	0.021
Ortalama	0.458	1.73	4.99	10.5	43.3	54.9	17.9	4.34	0.774	0.326	0.050	0.316
LT/SN/Km2	0.365	1.38	3.98	8.39	34.6	43.7	14.3	3.46	0.617	0.260	0.039	0.252
AKIM mm.	0.979	3.58	10.7	22.5	83.6	117.	36.9	9.28	1.60	0.697	0.106	0.654
MİL. M3	1.23	4.49	13.4	28.2	105.	147.	46.3	11.6	2.01	0.874	0.133	0.820

SU YILI (2006) YILLIK TOPLAM AKIM 361.06 MİLYON M3 288 MM. 9.1 LT/SN/Km2

03. Susurluk Havzasi

D03A043 SİMAV ÇAYI ÇAYGÖREN BARAJI-DOLUSAVAK

YERİ : Sındırgı-Çaygören Barajı Çıkışındadır.
28°12'19" Doğu - 39°16'44" Kuzey

YAĞIŞ ALANI : 1510.00 km2 YAKLAŞIK KOT : 215 m

GÖZLEM SÜRESİ : 02.01.1976 - 30.09.2006

ORTALAMA AKIMLAR : Gözlem süresinde 8.214 m3/sn. (9 Yıllık) 2006 Su yılında 10.389 m3/sn.

ANLIK EN ÇOK VE EN AZ AKIMLAR:

2006 Su yılında anlık ençok akım	:	57.4	m3/sn	13.03.2006
2006 Su yılında anlık enaz akım	:	0.120	m3/sn	30.11.2005
Gözlem süresinde anlık ençok akım	:	175.	m3/sn	19.12.1981
Gözlem süresinde anlık enaz akım	:	0.000	m3/sn	13.04.1982

Akımlar 01 Ekim 2005 'den 30 Eylül 2006' a kadar m3/sn olarak

Gün	Ekim	Kasım	Aralık	Ocak	Şubat	Mart	Nisan	Mayıs	Haziran	Temmuz	Ağustos	Eylül
01	2.72	1.25	0.120	0.120	0.120	52.8	9.55	5.86	5.86	6.59	13.9	8.76
02	3.28	0.860	0.120	0.120	0.120	52.0	9.98	5.86	5.50	9.12	13.9	8.40
03	2.50	0.860	0.120	0.120	0.120	51.2	18.5	6.22	5.50	9.12	13.9	8.40
04	2.05	0.860	0.120	0.120	0.120	51.2	22.9	6.22	5.50	9.12	13.4	8.40
05	2.05	0.860	0.120	0.120	0.120	51.2	22.9	6.22	7.67	9.12	13.9	8.40
06	2.05	1.05	0.120	0.120	0.120	50.5	22.9	6.22	9.55	9.12	13.4	8.03
07	1.82	1.05	0.120	0.120	0.120	49.7	22.9	6.22	9.12	11.3	13.4	8.03
08	1.42	0.670	0.120	0.120	0.120	49.7	22.9	6.22	9.12	11.3	13.4	8.03
09	1.42	0.230	0.120	0.120	0.120	49.7	22.9	5.50	5.50	9.55	13.4	8.03
10	1.60	0.120	0.120	0.120	0.120	49.7	22.9	4.67	6.59	9.55	13.4	8.03
11	1.42	0.120	0.120	0.120	0.120	48.9	22.9	7.67	5.86	9.98	12.1	8.03
12	1.42	0.120	0.120	0.120	0.230	53.7	22.4	11.3	5.86	9.55	14.4	7.67
13	1.42	0.120	0.120	0.120	19.6	52.8	24.0	11.3	5.22	9.55	14.9	7.67
14	1.42	0.120	0.120	0.120	45.8	51.2	25.3	11.3	4.94	9.55	13.4	6.95
15	1.42	0.120	0.120	0.120	45.8	52.8	25.3	12.1	3.28	9.98	14.9	6.95
16	1.42	0.120	0.120	0.120	45.8	53.7	25.3	14.4	2.72	9.55	13.9	6.95
17	1.42	0.120	0.120	0.120	45.8	53.7	12.1	14.4	3.00	10.4	13.4	6.95
18	1.42	0.120	0.120	0.120	47.3	53.7	6.95	14.9	2.72	10.4	13.4	6.95
19	1.42	0.120	0.120	0.120	48.1	53.7	7.31	15.4	5.50	9.98	13.0	6.95
20	1.42	0.120	0.120	0.120	31.2	37.5	7.67	15.4	6.22	9.98	12.5	6.95
21	1.42	0.120	0.120	0.120	23.5	28.6	7.67	15.4	6.22	10.4	12.1	6.22
22	1.42	0.120	0.120	0.120	23.5	28.6	7.67	15.4	8.40	10.4	11.7	2.72
23	1.42	0.120	0.120	0.120	39.8	29.2	8.03	15.4	9.12	9.98	11.7	2.50
24	1.25	0.120	0.120	0.120	50.5	29.2	8.03	15.4	9.12	9.12	11.7	2.50
25	1.05	0.120	0.120	0.120	49.7	29.2	8.03	14.9	9.12	9.12	8.76	2.50
26	1.25	0.120	0.120	0.120	49.7	29.2	9.55	8.76	9.12	9.98	8.76	2.27
27	1.25	0.120	0.120	0.120	49.7	16.0	8.03	5.86	9.55	11.3	7.31	1.25
28	1.25	0.120	0.120	0.120	50.5	10.4	5.22	5.86	7.67	11.7	6.95	0.860
29	1.25	0.120	0.120	0.120	-----	8.76	5.22	5.86	8.03	10.8	6.95	0.510
30	1.25	0.120	0.120	0.120	-----	9.55	5.50	5.86	7.67	11.7	6.59	0.510
31	1.25	-----	0.120	0.120	-----	9.55	-----	5.86	-----	13.4	6.59	-----
Maks.	3.28	1.25	0.120	0.120	50.5	57.4	26.0	18.5	18.5	16.0	14.9	11.3
Min.	0.670	0.120	0.120	0.120	0.120	1.05	5.22	4.67	1.05	1.05	1.25	0.510
Ortalama	1.59	0.340	0.120	0.120	23.9	40.2	15.0	9.74	6.64	10.0	12.0	5.88
LT/SN/Km2	1.05	0.225	0.079	0.079	15.8	26.7	9.95	6.45	4.40	6.64	7.93	3.89
AKIM mm.	2.81	0.584	0.213	0.213	38.2	71.4	25.8	17.3	11.4	17.8	21.2	10.1
MİL. M3	4.25	0.882	0.321	0.321	57.7	108.	38.9	26.1	17.2	26.8	32.1	15.2

SU YILI (2006) YILLIK TOPLAM AKIM 327.77 MİLYON M3 217 MM. 6.9 LT/SN/Km2

03. Susurluk Havzasi

D03A044 Nilüfer Ç. Selahattin Saygi Brj.Giris

YERİ : Eski Orhaneli-Keles yolunun Orhaneli-Keles yol ayrımındakiköprünün 150 m. mansabında sağ sahildedir.
29°0'5" Doğu - 40°5'7" Kuzey

YAĞIŞ ALANI : 372,60 km2 YAKLAŞIK KOT : 341 m

GÖZLEM SÜRESİ : 01.09.1977 - 30.09.2006

ORTALAMA AKIMLAR : Gözlem süresinde 4.115 m3/sn. (24 Yıllık) 2006 Su yılında 5.370 m3/sn.

ANLIK EN ÇOK VE EN AZ AKIMLAR:

2006 Su yılında anlık ençok akım	:	55.4	m3/sn	11.02.2006
2006 Su yılında anlık enaz akım	:	0.028	m3/sn	06.08.2006
Gözlem süresinde anlık ençok akım	:	570.	m3/sn	18.12.1981
Gözlem süresinde anlık enaz akım	:	0.000	m3/sn	24.08.1989

İstasyon için kullanılmış anahtar bulunamadı.

Akımlar 01 Ekim 2005 'den 30 Eylül 2006' a kadar m3/sn olarak

Gün	Ekim	Kasım	Aralık	Ocak	Şubat	Mart	Nisan	Mayıs	Haziran	Temmuz	Ağustos	Eylül
01	0.907	1.28	5.69	14.5	3.64	19.9	13.0	8.72	3.64	1.74	0.217	0.150
02	0.907	1.28	4.90	9.65	4.06	19.0	12.3	7.80	4.06	1.47	0.217	0.150
03	1.74	1.28	4.48	6.87	4.06	31.6	12.3	6.87	4.06	1.47	0.150	0.150
04	1.28	1.28	4.48	6.48	4.06	22.6	13.0	6.48	3.64	1.47	0.150	0.150
05	1.09	1.28	4.48	6.08	4.06	19.0	13.0	6.87	2.80	1.47	0.150	0.150
06	1.09	1.28	4.48	6.08	5.69	17.5	13.0	6.48	2.53	1.28	0.150	0.150
07	1.09	1.28	3.22	5.29	5.69	17.5	13.0	6.48	2.53	1.09	0.150	0.150
08	1.09	1.28	3.22	4.90	4.90	17.5	12.3	6.48	2.53	1.09	0.150	0.150
09	0.907	1.28	3.64	4.48	4.90	16.0	13.0	6.48	2.80	0.907	0.088	0.150
10	0.907	1.28	3.22	4.48	11.5	14.5	13.8	6.08	3.22	0.907	0.088	0.150
11	0.907	1.28	2.80	4.48	29.8	14.5	13.8	5.69	2.80	0.720	0.088	0.150
12	1.09	1.28	2.80	4.06	23.5	28.0	13.8	5.69	2.80	0.720	0.088	0.150
13	1.09	1.28	2.80	4.06	11.5	21.7	17.5	6.08	2.80	0.720	0.088	0.150
14	1.09	1.28	2.80	4.06	8.72	22.6	16.0	5.69	3.22	0.720	0.088	0.150
15	1.09	1.28	2.53	3.64	6.87	19.9	13.8	6.08	2.80	1.09	0.088	0.150
16	1.09	1.28	3.22	3.64	6.08	18.3	13.8	6.08	2.80	0.907	0.088	0.150
17	1.09	1.09	4.48	3.22	6.08	17.5	13.8	6.08	2.80	0.720	0.088	0.217
18	1.09	1.74	4.90	3.22	6.87	15.3	13.8	6.08	2.80	0.720	0.088	0.217
19	1.09	2.53	12.3	5.69	9.65	14.5	13.0	5.69	2.53	0.720	0.088	0.217
20	1.09	5.69	6.48	5.69	13.0	13.8	13.8	5.69	2.27	0.720	0.088	0.438
21	1.09	3.22	4.90	4.48	13.8	12.3	13.0	5.69	2.00	0.720	0.150	0.438
22	1.09	3.22	4.48	4.48	13.8	11.5	11.5	5.69	1.74	0.532	0.088	0.532
23	1.09	2.27	4.48	4.48	13.8	12.3	10.6	5.69	1.47	0.532	0.088	0.907
24	1.09	3.22	4.48	4.48	13.8	13.8	10.6	5.29	1.47	0.532	0.088	0.907
25	1.09	5.69	4.06	4.48	19.0	13.8	10.6	4.90	1.47	0.438	0.088	0.907
26	1.09	14.5	4.06	4.06	21.7	13.0	9.65	4.48	1.28	0.438	0.088	0.907
27	1.09	13.0	4.06	4.06	22.6	13.0	8.72	4.48	1.47	0.532	0.088	0.907
28	0.907	8.72	4.90	3.64	20.8	13.0	8.72	4.48	2.00	0.532	0.088	0.907
29	1.09	6.87	10.6	3.64	-----	13.8	8.72	4.06	2.27	0.532	0.088	2.00
30	1.09	6.08	6.87	3.22	-----	13.8	8.72	4.06	2.00	0.532	0.088	2.27
31	1.09	-----	20.8	3.64	-----	13.0	-----	4.06	-----	0.532	0.088	-----
Maks.	2.27	28.9	39.6	19.9	55.4	48.7	19.0	8.72	5.69	19.9	0.297	4.90
Min.	0.720	1.09	2.53	3.22	3.64	10.6	7.80	4.06	1.09	0.297	0.028	0.150
Ortalama	1.08	3.28	5.18	5.01	11.2	16.9	12.4	5.82	2.55	0.855	0.110	0.472
LT/SN/Km2	2.90	8.80	13.9	13.4	30.1	45.4	33.3	15.6	6.85	2.29	0.296	1.27
AKIM mm.	7.78	22.8	37.2	36.0	72.8	122.	86.4	41.8	17.8	6.15	0.793	3.29
MİL. M3	2.90	8.49	13.9	13.4	27.1	45.3	32.2	15.6	6.62	2.29	0.295	1.22

SU YILI (2006) YILLIK TOPLAM AKIM 169.31 MİLYON M3 454 MM. 14.4 LT/SN/Km2

03. Susurluk Havzasi

D03A051 KÖTEYLİ DERESİ DEĞİRMENBOĞAZI

YERİ : BALIKESİR-DEĞİRMENBOĞAZI MESIRE YERININ KUZEY GIRIŞINDEDIR.
27°57'21" Doğu - 39°43'2" Kuzey

YAĞIŞ ALANI : 82.00 km2 YAKLAŞIK KOT : 120 m

GÖZLEM SÜRESİ : 01.10.1979 - 30.09.2006

ORTALAMA AKIMLAR : Gözlem süresinde 0.385 m3/sn. (25 Yıllık) 2006 Su yılında 0.392 m3/sn.

ANLIK EN ÇOK VE EN AZ AKIMLAR:

2006 Su yılında anlık ençok akım	:	40.0	m3/sn	11.02.2006
2006 Su yılında anlık enaz akım	:	0.000	m3/sn	09.10.2005
Gözlem süresinde anlık ençok akım	:	130.	m3/sn	05.12.1981
Gözlem süresinde anlık enaz akım	:	0.000	m3/sn	05.12.1984

7. Anahtar Eğrisi (Seviyeler cm olarak)

Seviye	Akım	Seviye	Akım	Seviye	Akım	Seviye	Akım
1	0.000	76	8.2	155	38.0	242	75.0
16	0.460	91	12.0	173	46.0	258	82.0
31	1.6	106	17.5	192	54.0	274	88.0
46	3.1	121	24.0	208	61.0	292	96.0
61	5.3	137	31.0	225	68.0	340	115.

Akımlar 01 Ekim 2005 'den 30 Eylül 2006' a kadar m3/sn olarak

Gün	Ekim	Kasım	Aralık	Ocak	Şubat	Mart	Nisan	Mayıs	Haziran	Temmuz	Ağustos	Eylül
01	0.001	0.014	0.056	0.280	0.400	0.720	0.460	0.093	0.056	0.006	0.029	KURU
02	0.001	0.014	0.056	0.210	0.460	0.660	0.460	0.093	0.029	0.003	0.014	KURU
03	0.014	0.014	0.029	0.140	0.540	1.10	0.400	0.093	0.029	0.003	0.006	KURU
04	0.029	0.014	0.029	0.140	0.660	0.660	0.400	0.140	0.056	0.006	0.006	KURU
05	0.006	0.014	0.029	0.093	0.780	0.590	0.400	0.140	0.056	0.006	0.003	KURU
06	0.003	0.014	0.029	0.093	3.30	0.540	0.400	0.093	0.056	0.006	0.001	KURU
07	0.001	0.014	0.029	0.093	1.85	0.870	0.340	0.093	0.056	0.006	0.006	KURU
08	0.001	0.014	0.029	0.093	1.50	5.00	0.280	0.093	0.056	0.006	0.029	KURU
09	KURU	0.014	0.056	0.093	1.35	2.10	0.460	0.093	0.056	0.014	0.014	KURU
10	KURU	0.014	0.029	0.093	7.30	1.35	0.400	0.093	0.056	0.006	0.014	KURU
11	KURU	0.014	0.029	0.140	14.0	1.85	0.340	0.093	0.056	0.006	0.006	KURU
12	KURU	0.014	0.029	0.140	3.60	2.60	0.280	0.093	0.029	0.006	0.006	KURU
13	KURU	0.014	0.029	0.093	1.95	1.40	0.280	0.093	0.029	0.006	0.006	KURU
14	KURU	0.014	0.029	0.093	1.40	11.5	0.280	0.093	0.029	0.029	0.029	KURU
15	KURU	0.014	0.029	0.093	1.15	3.50	0.280	0.093	0.029	0.056	0.014	KURU
16	KURU	0.014	0.029	0.093	1.10	1.65	0.280	0.093	0.029	0.029	0.006	KURU
17	KURU	0.014	0.029	0.093	1.00	1.25	0.280	0.093	0.029	0.029	0.006	KURU
18	KURU	0.014	0.029	0.093	3.10	3.30	0.280	0.093	0.029	0.014	0.014	KURU
19	0.001	0.029	1.35	0.280	2.20	3.10	0.210	0.093	0.029	0.014	0.006	KURU
20	0.006	0.029	0.540	1.10	1.55	1.35	0.210	0.093	0.029	0.014	0.029	KURU
21	0.006	0.093	0.280	0.540	1.10	1.00	0.140	0.093	0.014	0.029	0.014	KURU
22	0.006	0.056	0.140	0.400	0.940	0.780	0.140	0.093	0.006	0.014	0.003	KURU
23	0.006	0.029	0.093	1.10	0.780	0.720	0.140	0.140	0.006	0.014	0.003	KURU
24	0.006	0.029	0.093	0.460	0.660	0.870	0.140	0.093	0.014	0.014	0.003	KURU
25	0.006	0.093	0.093	0.400	4.30	0.870	0.140	0.093	0.006	0.006	0.006	KURU
26	0.006	0.280	0.093	0.400	3.20	0.780	0.140	0.093	0.006	0.006	0.006	KURU
27	0.006	0.210	0.056	0.460	1.50	0.720	0.140	0.093	0.006	0.006	0.006	KURU
28	0.006	0.093	0.056	0.460	0.940	0.720	0.093	0.093	0.006	0.006	0.003	KURU
29	0.006	0.056	0.093	0.400	-----	0.660	0.093	0.056	0.006	0.014	0.001	0.056
30	0.006	0.056	0.093	0.400	-----	0.590	0.093	0.093	0.006	0.029	0.001	0.093
31	0.014	-----	0.280	0.400	-----	0.590	-----	0.093	-----	0.029	KURU	-----
Maks.	0.093	0.460	5.90	3.00	40.0	36.0	0.460	0.140	0.093	0.093	0.093	0.280
Min.	KURU	0.014	0.029	0.093	0.400	0.460	0.093	0.056	0.006	0.003	0.001	KURU
Ortalama	0.004	0.044	0.125	0.289	2.24	1.72	0.266	0.096	0.030	0.014	0.009	0.005
LT/SN/Km2	0.054	0.530	1.52	3.53	27.3	21.0	3.24	1.18	0.365	0.170	0.114	0.061
AKIM mm.	0.144	1.38	4.07	9.45	66.0	56.3	8.41	3.15	0.947	0.455	0.306	0.157
MİL. M3	0.012	0.113	0.334	0.775	5.41	4.61	0.689	0.258	0.078	0.037	0.025	0.013

SU YILI (2006) YILLIK TOPLAM AKIM 12.35 MİLYON M3 151 MM. 4.8 LT/SN/Km2

03. Susurluk Havzasi

D03A052 DURSUNBEY ÇAYI SİNDERLER

YERİ : DURSUNBEY TAVŞANLI YOLU 13. KM SİNDE SİNDEL MAHALLESİNDEKİ BETON KÖPRÜDEDİR.
28°43'40" Doğu - 39°37'35" Kuzey

YAĞIŞ ALANI : 975.20 km2 YAKLAŞIK KOT : 294 m

GÖZLEM SÜRESİ : 01.10.1980 - 30.09.2006

ORTALAMA AKIMLAR : Gözlem süresinde 4.882 m3/sn. (25 Yıllık) 2006 Su yılında 6.870 m3/sn.

ANLIK EN ÇOK VE EN AZ AKIMLAR:

2006 Su yılında anlık ençok akım	:	190.	m3/sn	11.02.2006
2006 Su yılında anlık enaz akım	:	0.080	m3/sn	28.08.2006
Gözlem süresinde anlık ençok akım	:	820.	m3/sn	06.01.1981
Gözlem süresinde anlık enaz akım	:	0.000	m3/sn	29.07.1989

17. Anahtar Eğrisi (Seviyeler cm olarak)

Seviye	Akım	Seviye	Akım	Seviye	Akım	Seviye	Akım
28	0.105	58	2.4	250	174.	350	348.
35	0.200	70	5.5	280	216.	370	385.
40	0.360	90	14.2	290	229.	390	422.
46	0.740	110	26.0	310	274.	420	480.
54	1.6	150	58.0	330	311.	440	520.

Akımlar 01 Ekim 2005 'den 30 Eylül 2006' a kadar m3/sn olarak

Gün	Ekim	Kasım	Aralık	Ocak	Şubat	Mart	Nisan	Mayıs	Haziran	Temmuz	Ağustos	Eylül
01	0.552	0.716	2.74	22.4	5.55	32.1	11.9	4.78	1.48	0.498	0.145	0.110
02	0.552	0.661	2.24	12.3	6.25	27.5	11.0	4.78	1.48	0.245	0.162	0.217
03	0.607	0.661	2.02	8.74	6.61	48.2	10.5	4.52	1.39	0.300	0.145	0.217
04	0.661	0.716	1.80	6.61	7.32	44.7	10.5	4.25	1.30	0.716	0.162	0.217
05	0.661	0.770	1.70	5.55	7.67	27.5	10.5	3.98	1.22	0.661	0.145	0.190
06	0.661	0.770	1.48	5.78	12.3	23.5	9.60	3.98	1.30	0.607	0.162	0.145
07	0.607	0.770	1.48	5.78	24.8	21.5	9.23	3.98	1.30	0.498	0.145	0.110
08	0.607	0.846	1.37	5.31	17.1	28.1	8.85	4.25	1.39	0.498	0.127	0.145
09	0.552	0.846	1.48	4.84	12.8	26.8	8.85	4.25	1.48	0.419	0.127	0.162
10	0.552	0.770	1.70	4.37	13.7	22.2	8.48	3.98	1.82	0.419	0.127	0.162
11	0.607	0.770	1.59	3.73	141.	21.5	8.10	3.71	1.99	0.419	0.127	0.190
12	0.607	0.770	1.37	3.40	69.9	92.3	7.73	3.45	0.770	0.419	0.162	0.190
13	0.607	0.846	1.26	3.07	35.1	60.4	7.35	4.52	0.716	0.379	0.145	0.217
14	0.661	0.770	1.26	2.90	24.2	46.5	7.35	4.25	0.716	0.379	0.162	0.217
15	0.661	0.770	1.26	2.57	18.4	39.5	8.10	3.71	0.716	0.419	0.190	0.245
16	0.661	0.770	1.48	2.41	12.8	30.8	6.98	5.32	0.770	0.340	0.190	0.245
17	0.661	0.846	2.57	2.13	12.4	25.5	6.60	3.98	0.770	0.300	0.145	0.245
18	0.661	0.922	5.78	2.13	21.5	21.5	6.60	3.71	0.716	0.245	0.127	0.245
19	0.661	1.80	35.8	2.41	41.2	22.8	5.85	3.45	0.661	0.190	0.127	0.217
20	0.661	2.13	14.2	18.3	42.1	19.0	5.85	3.18	0.661	0.190	0.127	0.245
21	0.661	3.73	7.67	10.4	38.6	16.6	5.85	2.84	0.716	0.217	0.127	0.300
22	0.661	2.24	5.55	8.74	31.4	15.4	5.85	2.84	0.661	0.190	0.127	0.419
23	0.661	1.70	4.84	8.74	28.8	14.8	5.85	2.50	0.661	0.162	0.110	0.340
24	0.661	1.80	4.37	8.38	25.5	16.0	5.85	2.33	0.607	0.162	0.110	0.379
25	0.661	3.73	3.73	7.32	34.3	19.0	5.58	2.33	0.552	0.145	0.092	0.379
26	0.661	20.6	3.40	6.96	52.5	16.6	5.32	2.16	0.552	0.145	0.092	0.379
27	0.661	11.8	3.57	6.25	45.6	14.8	5.05	1.99	0.458	0.145	0.092	0.379
28	0.661	8.38	4.84	5.31	36.0	13.7	4.78	1.82	0.419	0.145	0.092	0.379
29	0.661	4.84	6.25	5.55	-----	12.8	4.78	1.82	0.458	0.162	0.110	0.607
30	0.661	3.57	8.38	5.55	-----	12.4	5.05	1.65	0.498	0.145	0.127	2.03
31	0.552	-----	13.3	5.31	-----	12.8	-----	1.65	-----	0.127	0.127	-----
Maks.	0.716	37.2	60.0	35.1	190.	150.	12.4	6.98	3.18	0.770	0.245	2.35
Min.	0.498	0.661	1.26	1.80	5.55	11.9	4.78	1.48	0.419	0.092	0.080	0.092
Ortalama	0.633	2.68	4.85	6.56	29.5	27.3	7.46	3.42	0.941	0.319	0.134	0.317
LT/SN/Km2	0.649	2.75	4.98	6.72	30.2	28.0	7.65	3.50	0.965	0.327	0.137	0.325
AKIM mm.	1.74	7.12	13.3	18.0	73.1	75.0	19.8	9.39	2.50	0.876	0.368	0.844
MİL. M3	1.70	6.94	13.0	17.6	71.3	73.2	19.3	9.15	2.44	0.854	0.359	0.823

SU YILI (2006) YILLIK TOPLAM AKIM 216.67 MİLYON M3 222 MM. 7.0 LT/SN/Km2

03. Susurluk Havzasi

D03A054 Nilüfer Ç. Güneybayir

YERİ : Bursa keles yolunun 35.km. sindeki çiftlik evinin yanındasağ sahildedir.
29°2'0" Doğu - 40°3'0" Kuzey

YAĞIŞ ALANI : 307,60 km2 YAKLAŞIK KOT : 385 m

GÖZLEM SÜRESİ : 01.10.1981 - 30.09.2006

ORTALAMA AKIMLAR : Gözlem süresinde 3.855 m3/sn. (24 Yıllık) 2006 Su yılında 3.615 m3/sn.

ANLIK EN ÇOK VE EN AZ AKIMLAR:

2006 Su yılında anlık ençok akım	:	42.0	m3/sn	03.03.2006
2006 Su yılında anlık enaz akım	:	0.015	m3/sn	15.08.2006
Gözlem süresinde anlık ençok akım	:	410.	m3/sn	15.12.1981
Gözlem süresinde anlık enaz akım	:	0.000	m3/sn	12.07.1989

İstasyon için kullanılmış anahtar bulunamadı.

Akımlar 01 Ekim 2005 'den 30 Eylül 2006' a kadar m3/sn olarak

Gün	Ekim	Kasım	Aralık	Ocak	Şubat	Mart	Nisan	Mayıs	Haziran	Temmuz	Ağustos	Eylül
01	0.270	0.270	0.380	9.70	1.70	15.0	11.0	7.10	3.10	1.50	0.105	0.046
02	0.480	0.270	0.380	6.40	1.70	14.0	9.70	6.80	3.40	1.15	0.105	0.105
03	1.15	0.270	0.380	5.00	1.90	28.0	11.0	6.80	3.40	1.15	0.105	0.046
04	0.480	0.270	0.380	4.30	1.90	18.6	11.0	6.40	3.10	1.30	0.105	0.046
05	0.480	0.270	0.380	4.00	1.90	14.5	11.0	6.40	2.60	1.15	0.105	0.046
06	0.380	0.380	0.380	3.70	3.70	13.0	11.5	6.00	2.30	0.950	0.046	0.046
07	0.380	0.380	0.380	3.40	3.40	12.5	11.0	6.00	2.30	0.780	0.046	0.046
08	0.380	0.380	0.380	3.10	2.90	12.5	10.0	5.60	2.30	0.620	0.046	0.046
09	0.380	0.380	0.380	2.90	2.60	11.0	11.0	5.60	2.90	0.620	0.046	0.046
10	0.270	0.380	0.380	2.60	4.70	9.40	12.0	5.00	2.90	0.480	0.046	0.046
11	0.270	0.380	0.380	2.30	19.5	9.40	12.0	4.70	2.60	0.480	0.046	0.046
12	0.270	0.380	0.380	2.10	9.00	23.0	11.5	5.00	2.60	0.380	0.046	0.105
13	0.950	0.380	0.380	2.10	6.00	16.5	14.5	5.30	2.60	0.380	0.046	0.046
14	0.270	0.380	0.380	1.90	5.00	17.0	14.0	5.00	2.90	0.480	0.105	0.105
15	0.270	0.380	0.380	1.90	4.30	14.5	12.5	5.30	2.60	0.480	0.046	0.105
16	0.270	0.380	0.380	1.70	3.70	13.0	12.0	5.30	2.90	0.480	0.015	0.105
17	0.270	0.380	0.380	1.70	3.70	11.5	12.0	5.00	2.60	0.380	0.046	0.105
18	0.270	0.380	0.380	1.50	4.30	10.0	12.0	5.00	2.60	0.270	0.046	0.105
19	0.270	0.380	0.380	3.40	5.60	9.40	11.5	5.00	2.30	0.270	0.046	0.270
20	0.270	0.380	5.30	3.10	7.60	8.50	11.5	5.00	2.10	0.480	0.046	0.270
21	0.270	0.380	0.380	2.30	8.50	9.40	10.0	5.00	1.70	0.270	0.015	0.270
22	0.270	0.380	0.380	2.10	8.50	7.60	9.70	5.00	1.50	0.270	0.015	0.380
23	0.270	0.380	0.380	2.10	9.00	8.50	9.40	4.70	1.30	0.270	0.015	0.380
24	0.270	0.380	1.30	1.90	9.00	9.70	9.40	4.30	1.30	0.270	0.015	0.480
25	0.270	0.380	2.10	2.10	15.0	9.40	9.00	4.00	1.15	0.185	0.015	0.620
26	0.950	0.380	1.90	1.90	18.0	9.00	8.10	4.30	1.15	0.105	0.015	0.620
27	0.270	0.380	2.10	1.70	18.0	9.00	7.60	4.00	1.15	0.105	0.015	0.620
28	0.270	0.380	2.90	1.70	15.5	9.40	7.60	3.40	1.70	0.105	0.015	0.620
29	0.270	0.380	7.60	1.50	-----	9.40	7.60	3.10	2.10	0.105	0.046	1.90
30	0.270	5.00	5.30	1.50	-----	11.5	7.10	3.10	1.70	0.105	0.046	1.90
31	0.270	-----	16.0	1.70	-----	11.0	-----	3.40	-----	0.105	0.105	-----
Maks.	2.30	5.00	32.0	14.0	36.0	42.0	17.0	7.10	4.00	1.70	0.105	4.70
Min.	0.270	0.270	0.380	1.30	1.70	6.80	6.80	2.60	0.950	0.105	0.015	0.015
Ortalama	0.377	0.516	1.71	2.82	7.02	12.4	10.6	5.05	2.30	0.506	0.050	0.319
LT/SN/Km2	1.22	1.68	5.54	9.16	22.8	40.4	34.5	16.4	7.46	1.64	0.164	1.04
AKIM mm.	3.28	4.35	14.8	24.5	55.2	108.	89.4	44.0	19.3	4.40	0.438	2.69
MİL. M3	1.01	1.34	4.57	7.54	17.0	33.3	27.5	13.5	5.95	1.35	0.135	0.827

SU YILI (2006) YILLIK TOPLAM AKIM 114.02 MİLYON M3 371 MM. 11.8 LT/SN/Km2

03. Susurluk Havzasi

D03A056 Sultaniye D. Sultaniye

YERİ : **Bursa Orhaneli yolunun 20. km. sindeki eski kemer köprünün50.0 m. mansabındadır**

28°56'28" Doğu - 40°5'57" Kuzey

YAĞIŞ ALANI : **38,40 km2** **YAKLAŞIK KOT : 368 m**

GÖZLEM SÜRESİ : **16.09.1981 - 30.09.2006**

ORTALAMA AKIMLAR : **Gözlem süresinde 0.576 m3/sn. (23 Yıllık) 2006 Su yılında 0.629 m3/sn.**

ANLIK EN ÇOK VE EN AZ AKIMLAR:

2006 Su yılında anlık ençok akım	:	**14.5**	**m3/sn**	**11.02.2006**
2006 Su yılında anlık enaz akım	:	**0.001**	**m3/sn**	**31.08.2006**
Gözlem süresinde anlık ençok akım	:	**54.0**	**m3/sn**	**18.10.1989**
Gözlem süresinde anlık enaz akım	:	**0.000**	**m3/sn**	**05.10.1985**

İstasyon için kullanılmış anahtar bulunamadı.

Akımlar 01 Ekim 2005 'den 30 Eylül 2006' a kadar m3/sn olarak

Gün	Ekim	Kasım	Aralık	Ocak	Şubat	Mart	Nisan	Mayıs	Haziran	Temmuz	Ağustos	Eylül
01	0.038	0.140	0.460	2.10	0.970	2.40	1.10	0.400	0.065	0.065	0.038	0.038
02	0.038	0.140	0.460	1.60	0.970	2.10	1.10	0.400	0.065	0.065	0.038	0.038
03	0.065	0.140	0.460	1.23	0.970	2.10	1.10	0.400	0.065	0.065	0.038	0.065
04	0.065	0.140	0.400	1.10	0.970	2.10	1.10	0.400	0.065	0.065	0.038	0.038
05	0.065	0.140	0.400	0.970	1.10	1.80	1.10	0.400	0.038	0.065	0.038	0.038
06	0.065	0.140	0.320	0.970	1.80	1.60	1.10	0.400	0.038	0.065	0.038	0.038
07	0.065	0.140	0.250	0.870	2.10	1.50	1.10	0.400	0.038	0.065	0.038	0.038
08	0.065	0.140	0.250	0.870	1.80	1.60	1.10	0.320	0.038	0.065	0.038	0.038
09	0.065	0.140	0.320	0.760	1.50	1.50	1.10	0.320	0.097	0.065	0.038	0.038
10	0.065	0.097	0.250	0.760	3.20	1.50	1.10	0.320	0.097	0.065	0.038	0.038
11	0.065	0.097	0.250	0.760	9.00	2.30	1.10	0.320	0.065	0.065	0.038	0.038
12	0.065	0.097	0.250	0.660	4.00	4.20	1.10	0.320	0.038	0.065	0.038	0.016
13	0.065	0.097	0.250	0.660	2.80	1.35	0.760	0.250	0.038	0.065	0.038	0.016
14	0.065	0.097	0.250	0.660	2.10	2.60	0.560	0.190	0.038	0.065	0.038	0.016
15	0.065	0.097	0.250	0.660	1.80	2.40	0.560	0.140	0.065	0.065	0.038	0.016
16	0.065	0.097	0.320	0.660	1.50	2.30	0.560	0.190	0.097	0.065	0.038	0.016
17	0.038	0.097	0.460	0.660	1.35	2.10	0.560	0.140	0.097	0.038	0.038	0.016
18	0.038	0.140	0.460	0.660	2.40	1.95	0.460	0.140	0.065	0.038	0.038	0.016
19	0.038	0.190	0.870	1.50	3.30	1.95	0.460	0.140	0.038	0.038	0.038	0.016
20	0.038	0.660	0.760	2.30	4.00	1.80	0.460	0.140	0.038	0.038	0.038	0.016
21	0.038	0.560	0.760	1.60	3.50	1.60	0.460	0.140	0.038	0.038	0.016	0.016
22	0.038	0.460	0.760	1.50	3.20	1.35	0.460	0.097	0.038	0.038	0.016	0.016
23	0.038	0.460	0.760	1.35	2.60	1.35	0.460	0.097	0.038	0.038	0.038	0.038
24	0.038	1.35	0.660	1.23	2.40	1.23	0.460	0.097	0.038	0.065	0.038	0.038
25	0.038	1.23	0.660	1.23	2.40	1.23	0.460	0.097	0.016	0.065	0.038	0.038
26	0.038	2.80	0.560	0.970	3.20	1.23	0.400	0.097	0.038	0.038	0.038	0.038
27	0.038	1.35	0.970	0.970	3.30	1.10	0.400	0.097	0.065	0.038	0.038	0.038
28	0.038	0.970	2.40	0.870	3.20	1.10	0.400	0.065	0.065	0.038	0.038	0.038
29	0.065	0.760	2.40	0.870	-----	1.10	0.400	0.065	0.097	0.038	0.065	0.097
30	0.065	0.560	1.80	0.870	-----	1.10	0.400	0.065	0.065	0.038	0.038	0.097
31	0.097	-----	2.10	0.870	-----	1.10	-----	0.065	-----	0.038	0.038	-----
Maks.	0.190	5.10	3.50	4.60	14.5	5.20	1.10	0.400	0.097	0.065	0.065	0.190
Min.	0.038	0.097	0.250	0.320	0.970	1.10	0.320	0.065	0.016	0.038	0.001	0.016
Ortalama	0.054	0.451	0.694	1.06	2.55	1.76	0.729	0.217	0.056	0.054	0.037	0.035
LT/SN/Km2	1.40	11.7	18.1	27.5	66.4	45.9	19.0	5.64	1.46	1.40	0.975	0.905
AKIM mm.	3.76	30.4	48.4	73.7	161.	123.	49.2	15.1	3.79	3.74	2.61	2.35
MİL. M3	0.144	1.17	1.86	2.83	6.17	4.72	1.89	0.580	0.145	0.144	0.100	0.090

SU YILI (2006) YILLIK TOPLAM AKIM 19.84 MİLYON M3 517 MM. 16.4 LT/SN/Km2

03. Susurluk Havzasi

D03A064 Gölecik D. Gölecik

YERİ : Karacabey Bandırma yolunun 6. km. sinden gölecik köyüne sa-pılır.5 km. sonra köye varılır.istasyon köyün içindeki köp-
28°17'0" Doğu - 40°17'0" Kuzey

YAĞIŞ ALANI : 79,50 km2 YAKLAŞIK KOT : 207 m

GÖZLEM SÜRESİ : 01.10.1983 - 30.09.2006

ORTALAMA AKIMLAR : Gözlem süresinde 1.077 m3/sn. (23 Yıllık) 2006 Su yılında 1.283 m3/sn.

ANLIK EN ÇOK VE EN AZ AKIMLAR:

2006 Su yılında anlık ençok akım	:	33.0	m3/sn	26.02.2006
2006 Su yılında anlık enaz akım	:	0.000	m3/sn	18.07.2006
Gözlem süresinde anlık ençok akım	:	93.0	m3/sn	28.11.1985
Gözlem süresinde anlık enaz akım	:	0.000	m3/sn	17.06.1985

İstasyon için kullanılmış anahtar bulunamadı.

Akımlar 01 Ekim 2005 'den 30 Eylül 2006' a kadar m3/sn olarak

Gün	Ekim	Kasım	Aralık	Ocak	Şubat	Mart	Nisan	Mayıs	Haziran	Temmuz	Ağustos	Eylül
01	0.018	0.710	0.630	1.60	1.25	9.30	1.40	0.510	0.115	0.115	KURU	0.002
02	0.056	0.560	0.510	1.25	1.40	7.84	1.40	0.510	0.115	0.115	KURU	0.002
03	0.117	0.300	0.510	1.25	1.60	9.70	1.40	0.510	0.115	0.115	KURU	0.002
04	0.056	0.300	0.510	1.07	1.75	5.10	1.25	0.390	0.115	0.056	KURU	0.002
05	0.056	0.202	0.390	0.930	2.13	4.20	1.25	0.390	0.187	0.056	KURU	0.002
06	0.056	0.202	0.390	0.770	3.40	3.90	1.25	0.390	0.187	0.056	KURU	0.002
07	0.056	0.202	0.390	0.770	2.73	3.90	1.07	0.390	0.187	0.056	KURU	0.002
08	0.056	0.202	0.390	1.25	2.34	5.30	1.07	0.390	0.187	0.056	KURU	0.002
09	0.056	0.202	0.390	1.95	2.13	4.50	1.07	0.390	0.285	0.056	KURU	0.002
10	0.056	0.117	0.390	3.40	2.55	3.40	1.07	0.390	0.510	0.115	KURU	0.002
11	0.056	0.117	0.390	2.95	7.45	5.30	0.930	0.390	0.390	0.115	KURU	0.002
12	0.056	0.117	0.390	2.34	4.20	7.84	0.930	0.390	0.285	0.056	KURU	0.002
13	0.117	0.117	0.285	2.55	3.17	5.90	0.930	0.390	0.285	0.056	KURU	0.002
14	0.056	0.202	0.285	2.73	2.55	7.06	0.930	0.390	0.390	0.056	KURU	0.002
15	0.117	0.300	0.285	2.34	2.34	5.30	0.930	0.390	0.285	0.056	KURU	0.002
16	0.860	0.300	0.390	1.95	2.13	4.20	0.770	0.390	0.390	0.018	KURU	0.002
17	0.425	0.202	0.510	1.75	2.13	3.40	0.770	0.390	0.285	0.018	KURU	0.002
18	0.202	0.860	0.630	1.60	9.00	3.17	0.770	0.285	0.285	0.018	KURU	0.002
19	0.202	1.02	2.13	1.95	9.00	2.73	0.630	0.285	0.187	0.018	KURU	0.002
20	0.117	4.80	1.25	2.34	12.5	2.55	0.630	0.285	0.187	0.018	KURU	0.002
21	0.117	2.34	0.930	1.95	10.5	2.34	0.630	0.285	0.187	0.018	KURU	0.002
22	0.117	1.07	0.930	1.75	11.0	2.34	0.630	0.285	0.187	0.002	KURU	0.002
23	0.056	1.25	0.770	1.95	9.70	2.13	0.630	0.187	0.187	0.002	KURU	0.002
24	0.056	3.40	0.770	1.75	9.70	2.13	0.630	0.187	0.115	0.002	KURU	0.002
25	0.056	3.63	0.770	1.75	15.5	1.95	0.510	0.187	0.115	0.002	KURU	0.002
26	0.056	2.34	0.770	1.75	27.0	1.75	0.510	0.187	0.115	0.002	KURU	0.002
27	0.056	1.60	1.40	1.40	15.5	1.75	0.510	0.187	0.115	0.002	KURU	0.002
28	0.056	1.25	2.95	1.40	8.23	1.75	0.510	0.187	0.115	0.002	KURU	0.002
29	0.056	1.07	2.55	1.25	-----	1.60	0.510	0.187	0.115	0.002	KURU	0.002
30	0.710	0.770	1.75	1.25	-----	1.60	0.510	0.115	0.115	KURU	KURU	0.002
31	1.59	-----	1.95	1.25	-----	1.60	-----	0.115	-----	KURU	KURU	-----
Maks.	2.72	6.29	3.17	3.90	33.0	13.5	1.40	0.510	0.630	0.115	KURU	1.40
Min.	0.018	0.117	0.285	0.770	1.25	1.60	0.510	0.115	0.115	KURU	KURU	KURU
Ortalama	0.184	0.992	0.858	1.75	6.53	4.05	0.868	0.321	0.211	0.041	KURU	0.002
LT/SN/Km2	2.32	12.5	10.8	22.0	82.2	50.9	10.9	4.04	2.66	0.511	0.000	0.025
AKIM mm.	6.21	32.3	28.9	58.9	199.	136.	28.3	10.8	6.89	1.37	0.000	0.065
MİL. M3	0.494	2.57	2.30	4.68	15.8	10.8	2.25	0.860	0.548	0.109	0.000	0.005

SU YILI (2006) YILLIK TOPLAM AKIM 40.42 MİLYON M3 508 MM. 16.1 LT/SN/Km2

03. Susurluk Havzasi

D03A067 MÜRVETLER DERESİ MÜRVETLER SOL ANAKANAL

YERİ : 1985BANDIRMA-MANYAS yolunun Hayalar köyünden sola dönülür 2.Km.sinden sonra istasyona varılır.istasyon köprünün 50 m.man-
28°2'0" Doğu - 40°40'0" Kuzey

YAĞIŞ ALANI : 307.00 km2 YAKLAŞIK KOT : 23.50 m

GÖZLEM SÜRESİ : 01.02.1984 - 30.09.2006

ORTALAMA AKIMLAR : Gözlem süresinde 0.976 m3/sn. (16 Yıllık) 2006 Su yılında 1.349 m3/sn.

ANLIK EN ÇOK VE EN AZ AKIMLAR:

2006 Su yılında anlık ençok akım	:	39.5	m3/sn	11.02.2006
2006 Su yılında anlık enaz akım	:	0.000	m3/sn	23.07.2006
Gözlem süresinde anlık ençok akım	:	81.0	m3/sn	15.04.1984
Gözlem süresinde anlık enaz akım	:	0.000	m3/sn	13.07.1985

4. Anahtar Eğrisi (Seviyeler cm olarak)

Seviye	Akım	Seviye	Akım	Seviye	Akım	Seviye	Akım
1	0.000	21	0.000	54	1.6	350	57.0
5	0.000	25	0.000	70	3.2	400	70.0
9	0.000	29	0.011	110	8.3	500	96.0
13	0.000	33	0.092	150	14.7		
17	0.000	40	0.490	300	45.0		

Akımlar 01 Ekim 2005 'den 30 Eylül 2006' a kadar m3/sn olarak

Gün	Ekim	Kasım	Aralık	Ocak	Şubat	Mart	Nisan	Mayıs	Haziran	Temmuz	Ağustos	Eylül
01	0.062	0.087	0.700	0.990	1.58	5.12	1.58	0.895	0.305	0.062	KURU	KURU
02	0.062	0.087	0.600	0.800	1.58	4.05	1.58	0.895	0.210	0.027	KURU	0.001
03	0.062	0.087	0.500	0.700	1.94	3.70	1.50	0.895	0.210	0.008	KURU	KURU
04	0.062	0.087	0.400	0.600	2.12	3.18	1.50	0.800	0.210	KURU	KURU	KURU
05	0.062	0.087	0.400	0.600	2.47	2.83	1.42	0.800	0.149	KURU	KURU	KURU
06	0.062	0.087	0.400	0.500	3.35	2.47	1.18	0.800	0.210	0.001	KURU	0.008
07	0.062	0.087	0.400	0.500	3.88	2.47	1.18	0.800	0.210	0.008	KURU	0.008
08	0.062	0.087	0.400	0.700	3.53	6.56	1.18	0.800	0.305	KURU	KURU	0.008
09	0.062	0.087	0.600	1.09	3.35	5.60	1.30	0.800	0.500	KURU	KURU	0.001
10	0.039	0.087	0.600	1.18	6.80	5.84	1.18	0.800	0.400	0.015	KURU	0.003
11	0.039	0.087	0.400	1.42	25.6	6.56	1.18	0.800	0.305	KURU	KURU	0.003
12	0.039	0.087	0.305	1.76	12.3	7.28	1.09	0.800	0.305	0.003	KURU	0.008
13	0.039	0.087	0.305	1.42	7.28	4.64	0.990	0.700	0.305	0.015	KURU	0.015
14	0.039	0.087	0.210	1.94	5.36	9.88	0.990	0.700	0.305	KURU	KURU	0.039
15	0.039	0.087	0.210	1.50	4.23	10.9	0.990	0.700	0.305	0.003	KURU	0.039
16	0.039	0.062	0.210	1.18	3.88	5.84	0.990	0.600	0.400	0.015	KURU	0.039
17	0.062	0.062	0.210	1.09	3.70	4.64	0.990	0.600	0.305	0.015	KURU	0.039
18	0.062	0.062	0.305	0.990	16.7	4.23	0.990	0.500	0.305	0.039	KURU	0.039
19	0.062	0.062	4.23	1.18	18.4	7.52	0.895	0.600	0.305	KURU	KURU	0.039
20	0.062	0.149	1.94	4.23	13.6	4.23	0.895	0.600	0.210	KURU	KURU	0.062
21	0.062	0.895	1.18	2.47	9.20	3.53	0.895	0.500	0.210	KURU	KURU	0.062
22	0.062	0.600	0.895	1.76	8.00	3.18	0.895	0.400	0.210	0.015	KURU	0.210
23	0.062	0.500	0.800	2.47	6.80	2.83	0.895	0.400	0.149	KURU	KURU	0.305
24	0.062	0.800	0.800	2.12	6.08	2.83	0.990	0.500	0.087	KURU	KURU	0.305
25	0.062	1.30	0.700	1.58	12.9	3.53	1.09	0.500	0.062	KURU	KURU	0.305
26	0.062	2.95	0.600	1.50	11.6	2.83	0.990	0.400	0.039	KURU	KURU	0.305
27	0.062	1.58	0.990	1.50	8.24	2.47	0.990	0.500	0.062	KURU	KURU	0.305
28	0.062	1.30	1.30	1.58	5.60	2.29	0.990	0.400	0.087	KURU	KURU	0.305
29	0.062	0.990	0.990	1.58	-----	2.12	0.895	0.305	0.062	KURU	KURU	0.400
30	0.062	0.800	0.800	1.50	-----	1.94	0.895	0.305	0.062	KURU	KURU	0.990
31	0.062	-----	0.700	1.50	-----	1.76	-----	0.210	-----	KURU	KURU	-----
Maks.	0.062	4.30	9.54	6.32	39.5	24.9	1.76	1.18	0.500	0.087	KURU	1.58
Min.	0.039	0.062	0.087	0.500	1.50	1.76	0.895	0.087	0.015	KURU	KURU	KURU
Ortalama	0.057	0.447	0.745	1.42	7.50	4.41	1.10	0.623	0.226	0.007	KURU	0.128
LT/SN/Km2	0.185	1.46	2.43	4.62	24.4	14.4	3.60	2.03	0.737	0.024	0.000	0.417
AKIM mm.	0.496	3.78	6.50	12.4	59.1	38.5	9.32	5.43	1.91	0.064	0.000	1.08
MİL. M3	0.152	1.16	1.99	3.80	18.2	11.8	2.86	1.67	0.587	0.020	0.000	0.332

SU YILI (2006) YILLIK TOPLAM AKIM 42.57 MİLYON M3 139 MM. 4.4 LT/SN/Km2

03. Susurluk Havzasi

D03A076 KARADERE DADALAR

YERİ : İVRİNDI-KINIK KÖY YOLUNUN 2. KM SINDEKI KÖPRÜDEDIR
27°31'11" Doğu - 39°34'49" Kuzey

YAĞIŞ ALANI : 209.30 km2 YAKLAŞIK KOT : 200 m

GÖZLEM SÜRESİ : 01.10.1984 - 30.09.2006

ORTALAMA AKIMLAR : Gözlem süresinde 1.437 m3/sn. (19 Yıllık) 2006 Su yılında 1.707 m3/sn.

ANLIK EN ÇOK VE EN AZ AKIMLAR:

2006 Su yılında anlık ençok akım	:	119.	m3/sn	18.12.2005
2006 Su yılında anlık enaz akım	:	0.017	m3/sn	16.08.2006
Gözlem süresinde anlık ençok akım	:	290.	m3/sn	21.02.2000
Gözlem Süresinde anlık enaz akım	:	0.000	m3/sn	10.12.1997

6. Anahtar Eğrisi (Seviyeler cm olarak)

Seviye	Akım	Seviye	Akım	Seviye	Akım	Seviye	Akım
15	0.004	95	11.5	175	49.0	255	98.0
31	0.220	111	17.5	191	59.0	282	115.
47	0.880	127	25.0	207	68.0	333	155.
63	2.2	143	32.0	223	77.0	383	195.
79	6.1	159	41.0	239	88.0	466	260.

Akımlar 01 Ekim 2005 'den 30 Eylül 2006' a kadar m3/sn olarak

Gün	Ekim	Kasım	Aralık	Ocak	Şubat	Mart	Nisan	Mayıs	Haziran	Temmuz	Ağustos	Eylül
01	0.041	0.052	0.646	3.52	2.44	10.6	1.65	0.745	0.132	0.063	0.030	0.063
02	0.052	0.052	0.547	2.44	2.98	4.52	1.50	0.745	0.132	0.052	0.030	0.063
03	0.063	0.052	0.448	1.94	3.70	4.94	1.50	0.646	0.132	0.052	0.030	0.052
04	0.052	0.052	0.448	1.79	3.52	3.16	1.50	0.646	0.132	0.052	0.030	0.063
05	0.052	0.063	0.348	1.50	3.88	2.62	1.37	0.547	0.132	0.041	0.027	0.052
06	0.041	0.063	0.249	2.08	21.0	2.08	1.25	0.547	0.132	0.041	0.027	0.052
07	0.041	0.063	0.150	1.65	7.84	10.6	1.25	0.547	0.132	0.041	0.027	0.052
08	0.030	0.052	0.150	1.37	4.94	23.1	2.08	0.547	0.118	0.030	0.027	0.052
09	0.027	0.052	0.448	1.37	3.88	7.84	2.08	0.646	0.118	0.041	0.027	0.052
10	0.030	0.063	0.249	1.37	23.9	4.73	1.50	0.646	0.118	0.041	0.027	0.052
11	0.030	0.063	0.150	1.50	33.3	5.58	1.37	0.646	0.118	0.030	0.024	0.063
12	0.030	0.063	0.150	1.50	10.3	21.8	1.25	0.646	0.118	0.030	0.024	0.063
13	0.041	0.063	0.150	1.37	6.23	13.2	1.12	0.646	0.104	0.041	0.024	0.063
14	0.041	0.052	0.150	1.37	4.52	14.2	1.12	0.646	0.104	0.041	0.024	0.052
15	0.041	0.063	0.150	1.25	3.70	6.92	1.12	0.646	0.118	0.041	0.020	0.052
16	0.030	0.052	0.150	1.12	2.98	4.94	0.997	0.646	0.104	0.052	0.027	0.052
17	0.041	0.052	0.150	1.12	2.98	3.70	0.997	0.547	0.132	0.052	0.027	0.063
18	0.041	0.118	8.88	0.997	6.23	5.79	0.997	0.547	0.150	0.052	0.027	0.074
19	0.041	0.104	10.0	3.16	5.15	4.30	0.997	0.547	0.132	0.063	0.027	0.074
20	0.041	0.249	3.52	5.58	4.09	3.88	0.997	0.448	0.118	0.063	0.027	0.074
21	0.041	0.150	2.44	3.34	3.52	3.70	0.871	0.348	0.118	0.052	0.027	0.074
22	0.041	0.132	1.94	2.80	2.98	3.16	0.871	0.348	0.104	0.041	0.027	0.085
23	0.041	0.118	1.65	6.00	2.62	2.98	0.871	0.348	0.104	0.041	0.027	0.074
24	0.041	0.118	1.37	4.09	2.26	4.30	0.871	0.348	0.085	0.041	0.027	0.104
25	0.041	6.46	1.25	4.09	29.6	2.98	0.745	0.249	0.085	0.041	0.030	0.104
26	0.041	3.70	1.25	3.70	13.5	2.62	0.646	0.150	0.074	0.041	0.041	0.085
27	0.052	2.44	1.25	2.80	11.2	2.44	0.646	0.150	0.074	0.041	0.030	0.104
28	0.041	1.37	1.25	2.62	9.75	2.08	0.646	0.150	0.074	0.041	0.041	0.104
29	0.052	0.871	3.52	2.62	-----	1.94	0.745	0.150	0.063	0.041	0.041	0.249
30	0.052	0.646	3.34	2.44	-----	1.79	0.745	0.132	0.063	0.052	0.052	0.132
31	0.052	-----	4.94	2.26	-----	1.65	-----	0.132	-----	0.041	0.063	-----
Maks.	0.104	51.3	119.	19.0	81.3	81.9	5.58	0.997	0.249	0.063	0.074	0.348
Min.	0.027	0.052	0.150	0.745	1.94	1.25	0.348	0.118	0.063	0.020	0.017	0.030
Ortalama	0.042	0.582	1.66	2.41	8.32	6.07	1.14	0.475	0.111	0.045	0.030	0.077
LT/SN/Km2	0.201	2.78	7.91	11.5	39.8	29.0	5.46	2.27	0.529	0.215	0.145	0.366
AKIM mm.	0.537	7.20	21.2	30.9	96.2	77.7	14.2	6.08	1.37	0.575	0.388	0.949
MİL. M3	0.112	1.51	4.44	6.46	20.1	16.3	2.96	1.27	0.287	0.120	0.081	0.199

SU YILI (2006) YILLIK TOPLAM AKIM 53.84 MİLYON M3 257 MM. 8.2 LT/SN/Km2

03. Susurluk Havzasi

D03A081 MÜRVETLER DERESİ MÜRVETLER

YERİ : 1985BANDIRMADAN MANYAS İLÇESİNE GİRERKEN SOLA DÖNÜLEREK MÜRVET-LER KÖYÜNE GELİNİR İSTASYON KÖY İÇİNDEKİ KÖPRÜNÜN 5 M. 28°41'0" Doğu - 40°2'0" Kuzey

YAĞIŞ ALANI : 272.50 km2 YAKLAŞIK KOT : 31 m

GÖZLEM SÜRESİ : 01.10.1985 - 30.09.2006

ORTALAMA AKIMLAR : Gözlem süresinde 2.834 m3/sn. (6 Yıllık) 2006 Su yılında 2.885 m3/sn.

ANLIK EN ÇOK VE EN AZ AKIMLAR:

2006 Su yılında anlık ençok akım	:	92.0	m3/sn	18.02.2006
2006 Su yılında anlık enaz akım	:	0.060	m3/sn	08.09.2006
Gözlem süresinde anlık ençok akım	:	160.	m3/sn	29.11.1985
Gözlem süresinde anlık enaz akım	:	0.000	m3/sn	01.10.1985

6. Anahtar Eğrisi (Seviyeler cm olarak)

Seviye	Akım	Seviye	Akım	Seviye	Akım	Seviye	Akım
4	0.010	19	1.5	34	7.3	49	18.0
7	0.060	22	2.3	37	9.2	60	29.1
10	0.200	25	3.3	40	11.3	80	55.0
13	0.470	28	4.6	43	13.5	100	94.0
16	0.890	31	5.7	46	15.6		

Akımlar 01 Ekim 2005 'den 30 Eylül 2006' a kadar m3/sn olarak

Gün	Ekim	Kasım	Aralık	Ocak	Şubat	Mart	Nisan	Mayıs	Haziran	Temmuz	Ağustos	Eylül
01	0.198	0.474	0.934	2.20	3.40	8.70	3.25	1.52	0.612	0.290	0.106	0.106
02	0.198	0.382	0.842	1.73	3.55	6.39	3.10	1.52	0.612	0.290	0.106	0.106
03	0.198	0.336	0.796	1.41	3.93	5.45	2.95	1.41	0.612	0.244	0.106	0.106
04	0.198	0.336	0.704	1.30	4.50	4.69	2.95	1.41	0.612	0.244	0.106	0.106
05	0.198	0.336	0.658	1.19	4.88	4.31	2.80	1.30	0.612	0.244	0.106	0.106
06	0.244	0.336	0.658	1.09	6.63	3.93	2.65	1.30	0.612	0.198	0.106	0.106
07	0.244	0.336	0.612	1.09	6.63	3.93	2.50	1.30	0.520	0.198	0.106	0.106
08	0.244	0.336	0.612	1.84	6.39	13.2	2.50	1.30	0.520	0.244	0.106	0.106
09	0.244	0.336	0.934	2.50	5.92	9.60	2.80	1.19	0.750	0.244	0.106	0.152
10	0.244	0.336	0.934	2.80	10.5	10.8	2.65	1.19	0.612	0.244	0.106	0.152
11	0.244	0.336	0.796	3.25	73.6	12.2	2.50	1.09	0.612	0.244	0.106	0.152
12	0.244	0.336	0.704	3.55	28.6	14.2	2.35	1.09	0.520	0.244	0.106	0.152
13	0.244	0.336	0.658	3.25	15.2	7.57	2.20	1.19	0.520	0.244	0.106	0.152
14	0.198	0.336	0.520	3.93	10.5	29.6	2.20	1.09	0.520	0.244	0.106	0.152
15	0.198	0.336	0.566	3.25	7.80	21.4	2.20	1.09	0.520	0.244	0.106	0.152
16	0.244	0.336	0.566	2.65	6.86	10.2	2.05	0.980	0.566	0.244	0.106	0.244
17	0.244	0.382	0.566	2.35	6.86	7.57	1.94	0.980	0.566	0.244	0.106	0.244
18	0.244	0.474	0.750	2.05	47.6	7.10	1.84	0.980	0.520	0.244	0.106	0.244
19	0.244	0.520	10.8	3.25	51.8	14.2	1.84	0.980	0.520	0.244	0.106	0.244
20	0.244	0.980	3.93	8.70	33.2	6.86	1.84	0.934	0.474	0.198	0.106	0.244
21	0.244	1.84	2.65	4.69	20.3	5.69	1.84	0.934	0.474	0.152	0.106	0.290
22	0.244	0.980	2.05	3.93	15.9	5.07	1.73	0.934	0.428	0.152	0.106	0.612
23	0.244	0.842	1.84	5.26	12.8	4.69	1.73	0.888	0.382	0.152	0.106	0.474
24	0.244	2.05	1.62	4.31	10.5	4.69	1.73	0.888	0.382	0.152	0.106	0.428
25	0.244	2.95	1.41	3.55	34.5	5.45	1.62	0.888	0.336	0.152	0.106	0.474
26	0.244	8.40	1.30	3.25	26.8	4.50	1.62	0.842	0.290	0.152	0.106	0.428
27	0.244	3.10	2.35	3.40	16.9	4.12	1.62	0.796	0.290	0.152	0.106	0.428
28	0.244	2.05	2.80	3.55	9.90	3.93	1.52	0.796	0.290	0.152	0.152	0.428
29	0.244	1.52	2.05	3.55	-----	3.55	1.52	0.750	0.290	0.152	0.106	0.382
30	0.244	1.09	1.73	3.40	-----	3.40	1.52	0.704	0.290	0.106	0.106	1.84
31	0.382	-----	1.73	3.40	-----	3.25	-----	0.658	-----	0.106	0.106	-----
Maks.	0.428	19.1	35.0	16.9	92.0	83.1	3.25	1.52	0.980	0.474	0.336	3.55
Min.	0.152	0.336	0.290	1.09	3.40	3.25	1.52	0.658	0.290	0.106	0.106	0.060
Ortalama	0.238	1.09	1.58	3.09	17.4	8.07	2.19	1.06	0.495	0.207	0.107	0.297
LT/SN/Km2	0.874	4.00	5.81	11.3	63.7	29.6	8.02	3.90	1.82	0.759	0.394	1.09
AKIM mm.	2.34	10.4	15.6	30.3	154.	79.3	20.8	10.4	4.71	2.03	1.06	2.83
MİL. M3	0.638	2.83	4.24	8.27	42.0	21.6	5.66	2.84	1.28	0.554	0.288	0.770

SU YILI (2006) YILLIK TOPLAM AKIM 90.97 MİLYON M3 334 MM. 10.6 LT/SN/Km2

03. Susurluk Havzasi

D03A082 Kocadere Keçiler

YERİ : **BURSA-KARACABEY-BANDIRMA YOLU 18 KM SİNDEN SAĞA DÖNÜLÜR, 6 KM SONRA KEÇİLER KÖYÜNDEDIR**

28°11'15" Doğu - 40°18'17" Kuzey

YAĞIŞ ALANI : **40,63 km2** **YAKLAŞIK KOT : 65 m**

GÖZLEM SÜRESİ : **01.10.1985 - 30.09.2006**

ORTALAMA AKIMLAR : **Gözlem süresinde 0.757 m3/sn. (19 Yıllık) 2006 Su yılında 1.131 m3/sn.**

ANLIK EN ÇOK VE EN AZ AKIMLAR:

2006 Su yılında anlık ençok akım	:	**36.9**	**m3/sn**	**25.02.2006**
2006 Su yılında anlık enaz akım	:	**0.001**	**m3/sn**	**03.08.2006**
Gözlem süresinde anlık ençok akım	:	**70.0**	**m3/sn**	**10.06.1986**
Gözlem süresinde anlık enaz akım	:	**0.000**	**m3/sn**	**01.10.1985**

İstasyon için kullanılmış anahtar bulunamadı.

Akımlar 01 Ekim 2005 'den 30 Eylül 2006' a kadar m3/sn olarak

Gün	Ekim	Kasım	Aralık	Ocak	Şubat	Mart	Nisan	Mayıs	Haziran	Temmuz	Ağustos	Eylül
01	0.042	0.500	0.620	1.12	1.25	6.80	1.55	0.740	0.220	0.042	0.003	0.003
02	0.086	0.310	0.500	0.990	1.25	5.90	1.55	0.740	0.220	0.042	0.003	0.001
03	0.145	0.310	0.500	0.990	1.40	6.20	1.40	0.740	0.220	0.086	0.001	0.001
04	0.086	0.310	0.500	0.870	1.55	5.04	1.40	0.620	0.220	0.042	0.001	0.001
05	0.086	0.310	0.410	0.870	1.70	4.20	1.25	0.620	0.220	0.042	7.80	0.003
06	0.086	0.310	0.410	0.740	3.00	3.95	1.25	0.620	0.220	0.042	0.001	0.003
07	0.086	0.310	0.410	1.12	2.60	4.20	1.25	0.620	0.220	0.042	0.003	0.003
08	0.086	0.145	0.410	1.55	2.20	5.32	1.25	0.620	0.220	0.042	0.003	0.003
09	0.086	0.145	0.410	2.80	1.85	4.48	1.25	0.620	0.410	0.042	0.003	0.003
10	0.086	0.145	0.310	3.00	3.00	3.95	1.12	0.500	0.310	0.042	0.001	0.003
11	0.086	0.145	0.310	2.80	5.60	4.76	1.12	0.500	0.220	0.042	0.001	0.042
12	0.145	0.145	0.310	2.00	3.47	6.20	1.12	0.500	0.220	0.042	0.001	0.012
13	0.086	0.145	0.310	2.20	2.80	5.32	1.12	0.500	0.310	0.042	0.001	0.003
14	0.086	0.310	0.310	2.80	2.40	5.60	1.12	0.500	0.310	0.042	0.001	0.003
15	0.145	0.410	0.310	2.20	2.00	5.04	1.12	0.410	0.220	0.042	0.001	0.003
16	0.740	0.310	0.410	1.85	1.85	4.20	0.990	0.410	0.310	0.012	0.003	0.003
17	0.310	0.310	0.500	1.55	2.00	3.70	0.990	0.410	0.145	0.012	0.003	0.003
18	0.145	0.500	0.620	1.40	4.20	3.23	0.990	0.410	0.145	0.042	0.003	0.012
19	0.145	0.620	1.70	1.85	5.90	3.00	0.990	0.410	0.145	0.042	0.012	0.012
20	0.145	3.95	0.990	2.00	7.47	2.80	0.990	0.410	0.145	0.012	0.003	0.086
21	0.145	1.85	0.870	1.70	7.47	2.60	0.870	0.410	0.145	0.012	0.003	0.086
22	0.145	0.870	0.740	1.55	7.47	2.40	0.870	0.410	0.086	0.012	0.003	0.310
23	0.145	0.740	0.620	1.70	6.80	2.20	0.870	0.410	0.086	0.012	0.012	1.40
24	0.145	1.40	0.620	1.55	6.80	2.20	0.870	0.310	0.086	0.012	0.012	0.740
25	0.145	3.23	0.620	1.55	12.0	2.00	0.870	0.310	0.086	0.012	0.012	0.220
26	0.086	2.80	0.620	1.40	16.0	2.20	0.740	0.310	0.086	0.012	0.012	0.145
27	0.086	1.40	0.990	1.25	9.60	1.85	0.740	0.310	0.086	0.003	0.012	0.145
28	0.145	0.990	1.85	1.25	7.13	1.85	0.740	0.310	0.086	0.003	0.012	0.145
29	0.220	0.870	1.85	1.12	-----	1.70	0.740	0.310	0.042	0.003	0.012	0.310
30	0.500	0.740	1.40	1.12	-----	1.70	0.740	0.145	0.042	0.003	0.012	0.220
31	0.500	-----	1.25	1.12	-----	1.55	-----	0.145	-----	0.003	0.012	-----
Maks.	2.00	9.20	2.20	6.20	36.9	8.13	1.55	0.740	0.740	0.086	7.80	1.40
Min.	0.042	0.145	0.310	0.740	1.25	1.55	0.620	0.086	0.012	0.003	0.001	0.001
Ortalama	0.167	0.818	0.699	1.61	4.67	3.75	1.06	0.461	0.183	0.028	0.257	0.131
LT/SN/Km2	4.10	20.1	17.2	39.7	115.	92.2	26.1	11.3	4.50	0.699	6.32	3.22
AKIM mm.	11.0	52.2	46.1	106.	278.	247.	67.8	30.4	11.7	1.87	16.9	8.34
MİL. M3	0.447	2.12	1.87	4.32	11.3	10.0	2.75	1.23	0.474	0.076	0.688	0.339

SU YILI (2006) YILLIK TOPLAM AKIM 35.61 MİLYON M3 877 MM. 27.8 LT/SN/Km2

03. Susurluk Havzasi

D03A083 KOCADERE ESATLAR

YERİ : ÖRENCİK-TAVŞANLI YOLUNUN ESATLAR KÖYÜNE 25 M. MESAFEDEDİR.
29°37'0" Doğu - 39°20'0" Kuzey

YAĞIŞ ALANI : 847.00 km2 YAKLAŞIK KOT : 945 m

GÖZLEM SÜRESİ : 01.10.1985 - 30.09.2006

ORTALAMA AKIMLAR : Gözlem süresinde 4.806 m3/sn. (9 Yıllık) 2006 Su yılında 4.328 m3/sn.

ANLIK EN ÇOK VE EN AZ AKIMLAR:

2006 Su yılında anlık ençok akım	:	66.5	m3/sn	12.02.2006
2006 Su yılında anlık enaz akım	:	0.654	m3/sn	25.08.2006
Gözlem süresinde anlık ençok akım	:	147.	m3/sn	18.12.2001
Gözlem süresinde anlık enaz akım	:	0.654	m3/sn	25.08.2006

Akımlar 01 Ekim 2005 'den 30 Eylül 2006' a kadar m3/sn olarak

Gün	Ekim	Kasım	Aralık	Ocak	Şubat	Mart	Nisan	Mayıs	Haziran	Temmuz	Ağustos	Eylül
01	1.37	2.81	1.86	2.48	1.27	14.9	1.66	4.31	6.26	5.12	1.74	2.11
02	2.15	2.81	1.86	1.86	1.27	13.8	1.66	4.31	6.26	5.12	1.67	2.11
03	2.48	2.81	1.86	1.86	1.46	21.6	1.66	4.70	6.26	6.38	1.67	2.11
04	2.48	2.81	1.86	1.76	1.46	29.4	1.66	4.31	5.87	7.31	1.60	2.11
05	2.15	2.81	1.86	1.76	1.46	14.9	1.86	4.70	5.87	8.23	1.60	2.96
06	2.15	2.81	1.76	1.76	1.46	11.9	1.76	4.70	2.05	8.23	1.60	2.63
07	2.15	2.81	1.76	1.76	1.66	10.1	1.76	4.70	2.48	6.38	1.52	2.63
08	2.15	2.48	1.76	1.76	3.80	11.9	1.76	5.48	3.14	6.38	1.52	2.47
09	2.15	2.48	1.76	1.76	4.79	12.9	1.76	5.48	3.14	2.19	5.03	2.63
10	3.47	2.48	1.76	1.76	9.16	10.1	1.76	5.48	3.14	2.19	22.7	1.84
11	3.47	2.15	1.76	1.76	33.9	8.23	1.76	5.09	2.81	2.19	6.69	1.84
12	3.47	2.15	1.76	1.66	46.4	8.23	1.76	5.09	2.48	2.19	2.19	1.93
13	3.47	2.15	1.76	1.66	20.5	8.23	1.76	5.09	3.47	2.84	2.84	1.93
14	3.47	2.15	1.76	1.56	14.9	9.16	1.76	5.09	4.46	3.49	2.19	2.02
15	3.14	2.15	1.76	1.76	11.0	10.1	1.76	5.48	4.46	3.49	2.84	2.02
16	3.14	2.15	1.76	1.66	9.16	8.23	1.76	5.48	4.46	3.49	2.84	1.93
17	3.14	2.15	1.76	1.66	8.23	8.23	1.76	5.87	4.13	3.49	2.84	1.56
18	3.14	2.05	1.86	1.66	11.0	7.31	1.76	5.48	4.13	2.19	13.5	1.46
19	3.14	2.05	1.76	1.66	27.2	7.31	1.76	5.48	3.47	2.84	11.6	1.65
20	3.14	2.05	2.05	4.46	22.7	6.38	1.76	5.48	2.15	3.49	10.0	1.65
21	3.14	2.05	1.95	1.95	23.8	5.45	1.76	5.48	2.81	2.19	9.50	1.93
22	3.14	2.05	1.66	1.76	18.3	5.45	1.76	5.48	3.14	2.84	9.50	1.84
23	2.81	2.05	1.66	1.76	16.0	4.79	4.31	5.48	3.14	2.19	7.02	1.65
24	2.81	1.95	1.66	1.76	17.1	1.95	4.31	5.48	3.47	2.84	1.65	1.46
25	2.81	1.95	1.66	1.46	17.1	1.95	4.31	5.48	3.80	2.84	0.654	1.56
26	2.81	2.05	1.66	1.46	20.5	1.95	4.31	5.87	3.47	2.19	2.47	1.46
27	2.81	2.48	1.66	1.46	21.6	1.86	4.31	5.87	3.47	2.84	2.47	1.46
28	2.81	1.95	1.66	1.37	16.0	1.76	4.31	5.87	3.80	2.19	2.47	1.46
29	2.81	1.95	1.66	1.37	-----	1.76	4.31	5.87	5.12	2.12	2.47	1.46
30	2.81	1.86	1.86	1.27	-----	1.76	4.31	6.26	5.12	1.82	2.47	1.46
31	2.81	-----	1.76	1.27	-----	1.66	-----	6.90	-----	1.74	2.11	-----
Maks.	3.80	3.80	2.05	11.9	66.5	43.3	4.31	8.19	6.38	10.1	26.1	2.96
Min.	1.37	1.86	1.66	1.27	1.27	1.66	1.56	4.31	2.05	1.74	0.654	1.46
Ortalama	2.81	2.29	1.77	1.77	13.7	8.49	2.43	5.35	3.93	3.65	4.55	1.91
LT/SN/Km2	3.31	2.70	2.09	2.09	16.2	10.0	2.87	6.32	4.64	4.30	5.37	2.26
AKIM mm.	8.87	7.00	5.60	5.60	39.1	26.9	7.44	16.9	12.0	11.5	14.4	5.85
MİL. M3	7.52	5.93	4.75	4.74	33.1	22.7	6.30	14.3	10.2	9.77	12.2	4.95

SU YILI (2006) YILLIK TOPLAM AKIM 136.46 MİLYON M3 161 MM. 5.1 LT/SN/Km2

03. Susurluk Havzasi

D03A084 DEGİRMENCIK DERESI EYÜPBÜKÜ

YERİ : 1986KEPSUT-DURSUNBEY KARAYOLUNUN 7. KM.SINDEKI KOPRUNUN 100 M.MENBAI`NDADIR.
28°14'0" Doğu - 39°39'0" Kuzey

YAĞIŞ ALANI : 234.40 km2 YAKLAŞIK KOT : 160 m

GÖZLEM SÜRESİ : 01.10.1986 - 30.09.2006

ORTALAMA AKIMLAR : Gözlem süresinde 1.226 m3/sn. (20 Yıllık) 2006 Su yılında 1.429 m3/sn.

ANLIK EN ÇOK VE EN AZ AKIMLAR:

2006 Su yılında anlık ençok akım	:	90.0	m3/sn	11.03.2006
2006 Su yılında anlık enaz akım	:	0.128	m3/sn	05.10.2005
Gözlem süresinde anlık ençok akım	:	270.	m3/sn	16.12.1987
Gözlem süresinde anlık enaz akım	:	0.000	m3/sn	01.10.1986

5. Anahtar Eğrisi (Seviyeler cm olarak)

Seviye	Akım	Seviye	Akım	Seviye	Akım	Seviye	Akım
7	0.010	98	20.0	179	55.0	258	91.0
23	0.820	114	27.0	194	62.0	276	98.0
56	6.9	132	34.0	211	69.0	323	125.
70	11.0	147	41.0	227	76.0	376	155.
84	15.5	164	48.0	243	84.0		

Akımlar 01 Ekim 2005 'den 30 Eylül 2006' a kadar m3/sn olarak

Gün	Ekim	Kasım	Aralık	Ocak	Şubat	Mart	Nisan	Mayıs	Haziran	Temmuz	Ağustos	Eylül
01	0.170	0.220	0.520	3.60	1.41	5.00	1.53	0.710	0.290	0.220	0.170	0.170
02	0.170	0.220	0.430	2.17	1.53	4.00	1.41	0.710	0.290	0.220	0.170	0.170
03	0.170	0.220	0.360	1.53	1.53	10.5	1.28	0.710	0.290	0.220	0.170	0.170
04	0.170	0.220	0.360	1.28	1.53	5.55	1.28	0.710	0.290	0.220	0.170	0.170
05	0.128	0.220	0.290	1.16	2.17	4.00	1.28	0.710	0.220	0.220	0.170	0.170
06	0.128	0.220	0.220	1.16	10.5	3.16	1.16	0.710	0.290	0.220	0.170	0.170
07	0.128	0.220	0.220	1.16	5.38	4.20	1.16	0.615	0.290	0.220	0.170	0.170
08	0.128	0.220	0.290	1.16	3.80	6.60	1.16	0.615	0.290	0.220	0.170	0.170
09	0.128	0.220	0.615	1.03	3.16	4.60	1.16	0.615	0.360	0.220	0.170	0.170
10	0.128	0.220	0.430	0.940	8.90	4.20	1.16	0.615	0.710	0.220	0.170	0.170
11	0.170	0.220	0.360	0.940	32.0	13.0	1.03	0.520	0.430	0.170	0.170	0.170
12	0.170	0.170	0.290	0.820	10.0	19.0	1.03	0.430	0.360	0.128	0.128	0.170
13	0.170	0.220	0.290	0.820	5.73	7.20	1.03	0.710	0.290	0.128	0.170	0.170
14	0.170	0.220	0.290	0.710	4.40	11.5	1.03	0.710	0.360	0.128	0.220	0.170
15	0.170	0.220	0.290	0.615	3.38	7.20	1.03	0.615	0.360	0.128	0.220	0.170
16	0.170	0.220	0.710	0.615	2.72	5.55	1.03	0.615	0.360	0.128	0.220	0.170
17	0.170	0.220	1.68	0.520	2.50	4.80	0.940	0.615	0.290	0.128	0.220	0.170
18	0.170	0.220	1.16	0.360	5.55	5.20	0.940	0.520	0.290	0.170	0.220	0.170
19	0.170	0.220	3.38	8.00	6.40	5.20	0.940	0.520	0.290	0.170	0.170	0.170
20	0.170	0.615	2.00	7.80	6.40	4.20	0.820	0.520	0.290	0.170	0.170	0.170
21	0.170	0.520	1.84	3.60	5.55	3.60	1.16	0.520	0.290	0.170	0.128	0.290
22	0.170	0.360	1.53	2.50	4.80	2.94	1.03	0.430	0.290	0.170	0.128	0.220
23	0.170	0.290	1.03	3.80	4.20	2.50	0.940	0.430	0.220	0.170	0.128	0.170
24	0.170	0.360	0.940	2.33	3.80	2.33	0.820	0.430	0.220	0.170	0.128	0.220
25	0.170	2.17	0.940	2.17	5.73	2.17	0.820	0.360	0.220	0.170	0.128	0.290
26	0.170	5.00	0.940	2.00	8.30	2.00	0.820	0.360	0.220	0.170	0.128	0.220
27	0.170	2.50	1.16	1.84	13.0	1.84	0.710	0.360	0.220	0.170	0.128	0.220
28	0.170	1.28	2.17	1.68	6.40	1.68	0.710	0.360	0.220	0.170	0.128	0.220
29	0.170	0.820	2.17	1.68	-----	1.68	0.710	0.360	0.220	0.170	0.128	0.710
30	0.170	0.615	1.68	1.53	-----	1.68	0.820	0.360	0.220	0.170	0.128	0.360
31	0.220	-----	5.00	1.53	-----	1.84	-----	0.290	-----	0.170	0.128	-----
Maks.	0.220	5.00	19.0	50.0	54.0	90.0	1.53	0.820	1.41	0.220	0.220	0.710
Min.	0.128	0.170	0.220	0.360	1.41	1.41	0.710	0.290	0.128	0.128	0.128	0.128
Ortalama	0.163	0.622	1.08	1.97	6.10	5.13	1.03	0.540	0.299	0.178	0.162	0.211
LT/SN/Km2	0.697	2.65	4.62	8.40	26.0	21.9	4.40	2.31	1.28	0.759	0.690	0.899
AKIM mm.	1.87	6.88	12.4	22.5	62.9	58.6	11.4	6.18	3.31	2.03	1.85	2.33
MİL. M3	0.438	1.61	2.90	5.27	14.8	13.7	2.67	1.45	0.776	0.477	0.433	0.546

SU YILI (2006) YILLIK TOPLAM AKIM 45.07 MİLYON M3 192 MM. 6.1 LT/SN/Km2

03. Susurluk Havzasi

D03A085 Yaylacik D. Inegazi

YERİ : 1988BURSA İLİ ÇALI NAHİYESİNE GELİNİR 7 KM SONRA İNEGAZİ KÖYÜ-NE VARILIR.İSTASYON KÖYÜN 1 KM. MANSABINDADIR. (LİM)
28°52'15" Doğu - 40°8'16" Kuzey

YAĞIŞ ALANI : 13,40 km2 YAKLAŞIK KOT : 306 m

GÖZLEM SÜRESİ : 01.10.1987 - 30.09.2006

ORTALAMA AKIMLAR : Gözlem süresinde 0.217 m3/sn. (19 Yıllık) 2006 Su yılında 0.273 m3/sn.

ANLIK EN ÇOK VE EN AZ AKIMLAR:

2006 Su yılında anlık ençok akım	:	10.9	m3/sn	11.02.2006
2006 Su yılında anlık enaz akım	:	0.000	m3/sn	28.07.2006
Gözlem süresinde anlık ençok akım	:	21.8	m3/sn	10.04.1991
Gözlem süresinde anlık enaz akım	:	0.000	m3/sn	01.08.1988

İstasyon için kullanılmış anahtar bulunamadı.

Akımlar 01 Ekim 2005 'den 30 Eylül 2006' a kadar m3/sn olarak

Gün	Ekim	Kasım	Aralık	Ocak	Şubat	Mart	Nisan	Mayıs	Haziran	Temmuz	Ağustos	Eylül
01	0.008	0.029	0.138	1.00	0.300	1.24	0.255	0.084	0.016	0.008	0.001	KURU
02	0.005	0.008	0.111	0.707	0.353	1.00	0.255	0.084	0.016	0.005	0.001	KURU
03	0.008	0.008	0.138	0.520	0.353	1.00	0.255	0.063	0.016	0.008	0.001	KURU
04	0.008	0.016	0.111	0.407	0.353	0.840	0.255	0.063	0.016	0.008	0.001	KURU
05	0.008	0.016	0.111	0.353	0.407	0.707	0.255	0.063	0.016	0.005	0.001	KURU
06	0.005	0.029	0.084	0.300	0.773	0.580	0.255	0.063	0.016	0.005	0.001	KURU
07	0.005	0.063	0.084	0.300	0.840	0.580	0.255	0.063	0.016	0.005	KURU	KURU
08	0.005	0.029	0.084	0.300	0.707	0.640	0.255	0.063	0.063	0.005	KURU	KURU
09	0.005	0.029	0.084	0.300	0.640	0.580	0.255	0.063	0.063	0.005	KURU	KURU
10	0.005	0.029	0.084	0.300	2.50	0.580	0.210	0.063	0.042	0.005	KURU	KURU
11	0.005	0.029	0.084	0.300	4.90	1.16	0.210	0.063	0.042	0.005	KURU	KURU
12	0.005	0.029	0.084	0.255	2.30	2.00	0.210	0.063	0.029	0.005	KURU	KURU
13	0.005	0.029	0.084	0.255	1.65	1.32	0.210	0.063	0.063	0.001	KURU	KURU
14	0.005	0.029	0.063	0.255	1.24	1.08	0.210	0.063	0.063	0.005	KURU	KURU
15	0.005	0.029	0.063	0.210	1.00	1.00	0.210	0.063	0.042	0.001	KURU	KURU
16	0.008	0.029	0.111	0.210	0.840	1.00	0.210	0.063	0.042	0.001	KURU	KURU
17	0.008	0.016	0.165	0.165	0.707	0.920	0.165	0.063	0.042	0.001	0.001	KURU
18	0.005	0.063	0.165	0.165	1.75	0.840	0.111	0.063	0.042	0.001	0.001	KURU
19	0.008	0.111	0.300	0.640	2.50	0.773	0.111	0.063	0.029	0.001	KURU	KURU
20	0.008	0.640	0.300	1.00	2.60	0.707	0.084	0.063	0.029	0.001	KURU	KURU
21	0.008	0.353	0.255	0.773	2.20	0.640	0.084	0.063	0.029	0.001	KURU	KURU
22	0.008	0.165	0.255	0.580	1.90	0.580	0.084	0.016	0.016	0.001	KURU	KURU
23	0.005	0.255	0.210	0.580	1.65	0.520	0.084	0.029	0.008	0.001	KURU	KURU
24	0.005	1.00	0.210	0.460	1.49	0.460	0.084	0.029	0.008	0.001	KURU	KURU
25	0.005	0.840	0.210	0.407	1.57	0.460	0.084	0.029	0.008	0.001	KURU	KURU
26	0.005	0.773	0.210	0.407	1.80	0.407	0.084	0.029	0.008	0.001	KURU	KURU
27	0.005	0.460	0.580	0.353	1.80	0.353	0.084	0.029	0.005	0.001	KURU	KURU
28	0.005	0.353	1.65	0.353	1.65	0.300	0.084	0.029	0.008	0.001	KURU	KURU
29	0.008	0.255	1.32	0.300	-----	0.300	0.084	0.016	0.016	0.001	KURU	KURU
30	0.016	0.165	0.773	0.300	-----	0.300	0.084	0.016	0.008	0.001	KURU	KURU
31	0.042	-----	1.16	0.300	-----	0.300	-----	0.016	-----	0.001	KURU	-----
Maks.	0.255	1.80	2.60	1.80	10.9	3.00	0.300	0.300	2.00	0.008	0.001	KURU
Min.	0.005	0.008	0.063	0.165	0.300	0.300	0.084	0.008	0.005	KURU	KURU	KURU
Ortalama	0.008	0.196	0.299	0.411	1.46	0.747	0.169	0.052	0.027	0.003	0.000	KURU
LT/SN/Km2	0.568	14.6	22.3	30.7	109.	55.8	12.6	3.86	2.03	0.221	0.019	0.000
AKIM mm.	1.52	37.9	59.8	82.2	263.	149.	32.7	10.3	5.27	0.593	0.052	0.000
MİL. M3	0.020	0.508	0.802	1.10	3.52	2.00	0.439	0.138	0.071	0.008	0.001	0.000

SU YILI (2006) YILLIK TOPLAM AKIM 8.61 MİLYON M3 642 MM. 20.4 LT/SN/Km2

03. Susurluk Havzasi

D03A086 KOCADERE ADALİ

YERİ : ADALI KÖYÜNÜN 2 KM GÜNEYBATISINDA YAYA KÖPRÜSÜNDE TESİS EDILMIŞTIR.
28°15'49" Doğu - 39°23'46" Kuzey

YAĞIŞ ALANI : 63.00 km2 YAKLAŞIK KOT : 375 m

GÖZLEM SÜRESİ : 22.04.1987 - 30.09.2006

ORTALAMA AKIMLAR : Gözlem süresinde 0.481 m3/sn. (19 Yıllık) 2006 Su yılında 0.491 m3/sn.

ANLIK EN ÇOK VE EN AZ AKIMLAR:

2006 Su yılında anlık ençok akım	:	14.6	m3/sn	11.03.2006
2006 Su yılında anlık enaz akım	:	0.000	m3/sn	08.07.2006
Gözlem süresinde anlık ençok akım	:	26.2	m3/sn	23.12.2001
Gözlem süresinde anlık enaz akım	:	0.000	m3/sn	10.07.1988

6. Anahtar Eğrisi (Seviyeler cm olarak)

Seviye	Akım	Seviye	Akım	Seviye	Akım	Seviye	Akım
1	0.000	16	0.002	50	1.6	110	13.2
4	0.000	19	0.011	72	4.6	120	16.0
7	0.000	22	0.033	82	6.4	130	19.0
10	0.000	25	0.077	90	8.2	145	23.0
13	0.000	35	0.440	100	10.7	155	26.6

Akımlar 01 Ekim 2005 'den 30 Eylül 2006' a kadar m3/sn olarak

Gün	Ekim	Kasım	Aralık	Ocak	Şubat	Mart	Nisan	Mayıs	Haziran	Temmuz	Ağustos	Eylül
01	0.004	0.024	0.268	1.20	0.354	2.08	0.969	0.225	0.011	0.002	KURU	KURU
02	0.004	0.024	0.225	0.817	0.440	1.84	0.969	0.225	0.011	0.002	KURU	0.001
03	0.011	0.024	0.193	0.620	0.440	2.45	0.860	0.193	0.011	0.002	KURU	0.004
04	0.007	0.024	0.162	0.500	0.500	2.20	0.860	0.193	0.007	0.002	KURU	0.002
05	0.007	0.024	0.130	0.440	0.560	1.73	0.860	0.193	0.004	0.002	KURU	0.004
06	0.007	0.024	0.104	0.440	2.89	1.41	0.776	0.193	0.004	0.002	KURU	0.004
07	0.007	0.024	0.104	0.397	1.88	1.51	0.692	0.193	0.004	0.002	KURU	0.002
08	0.007	0.024	0.104	0.354	1.31	2.45	0.692	0.162	0.004	0.002	KURU	0.002
09	0.007	0.024	0.225	0.311	0.970	2.08	0.692	0.162	0.004	0.002	KURU	0.002
10	0.007	0.024	0.193	0.311	3.50	1.73	0.692	0.162	0.004	0.002	KURU	0.002
11	0.011	0.024	0.130	0.225	7.22	2.60	0.608	0.130	0.004	0.002	KURU	0.002
12	0.011	0.024	0.130	0.225	3.80	8.45	0.608	0.162	0.007	0.002	KURU	0.004
13	0.011	0.024	0.104	0.193	2.60	4.40	0.692	0.225	0.007	0.002	KURU	0.004
14	0.011	0.024	0.104	0.193	1.95	3.95	0.776	0.193	0.004	0.002	KURU	0.004
15	0.011	0.024	0.104	0.162	1.41	3.20	0.776	0.130	0.004	0.002	KURU	0.004
16	0.011	0.024	0.225	0.162	1.08	2.60	0.692	0.130	0.004	0.002	KURU	0.004
17	0.011	0.024	0.680	0.162	1.08	1.95	0.524	0.130	0.004	0.001	KURU	0.004
18	0.011	0.193	0.680	0.130	1.62	1.95	0.440	0.130	0.004	KURU	KURU	0.004
19	0.011	0.130	1.05	0.311	2.33	1.73	0.397	0.130	0.004	KURU	KURU	0.004
20	0.016	0.620	0.311	0.970	2.45	1.41	0.354	0.104	0.004	KURU	KURU	0.004
21	0.016	0.354	0.225	0.620	2.33	1.30	0.354	0.077	0.004	KURU	KURU	0.007
22	0.016	0.193	0.500	0.620	2.20	1.19	0.311	0.077	0.004	KURU	KURU	0.007
23	0.016	0.193	0.397	0.680	1.95	1.30	0.354	0.057	0.004	KURU	KURU	0.007
24	0.016	0.354	0.354	0.560	1.84	1.62	0.311	0.024	0.004	KURU	KURU	0.004
25	0.011	0.740	0.268	0.500	3.35	1.95	0.311	0.016	0.004	KURU	KURU	0.007
26	0.016	2.10	0.268	0.440	3.58	1.51	0.268	0.011	0.004	KURU	KURU	0.004
27	0.016	1.76	0.354	0.397	2.75	1.30	0.225	0.011	0.002	KURU	KURU	0.004
28	0.016	0.740	0.500	0.225	2.20	1.19	0.225	0.011	0.002	KURU	KURU	0.004
29	0.016	0.500	0.740	0.397	-----	1.08	0.225	0.011	0.002	KURU	KURU	0.130
30	0.016	0.397	0.740	0.354	-----	1.19	0.268	0.011	0.002	KURU	KURU	0.033
31	0.016	-----	1.20	0.500	-----	1.08	-----	0.011	-----	KURU	KURU	-----
Maks.	0.024	4.15	2.21	2.10	9.95	14.6	1.19	0.354	0.011	0.002	KURU	0.354
Min.	0.004	0.016	0.077	0.130	0.311	0.969	0.225	0.011	0.002	KURU	KURU	KURU
Ortalama	0.011	0.289	0.347	0.433	2.09	2.14	0.559	0.119	0.005	0.001	KURU	0.009
LT/SN/Km2	0.181	4.59	5.52	6.87	33.2	34.0	8.88	1.89	0.075	0.017	0.000	0.142
AKIM mm.	0.485	11.9	14.8	18.4	80.3	91.1	23.0	5.05	0.195	0.045	0.000	0.368
MİL. M3	0.031	0.750	0.931	1.16	5.06	5.74	1.45	0.318	0.012	0.003	0.000	0.023

SU YILI (2006) YILLIK TOPLAM AKIM 15.48 MİLYON M3 246 MM. 7.8 LT/SN/Km2

03. Susurluk Havzasi

D03A089 Orhaneli Ç. Çaltilibük

YERİ : BURSA İLİ M.KEMALPAŞA İLÇESİ ÇALTILIBÜK NAHİYESİ KÖYİÇİKARAYOLU KÖPRÜSÜNÜN 25 M. MENBAINDADIR.
29°6'0" Doğu - 39°56'49" Kuzey

YAĞIŞ ALANI : 4591,00 km2 YAKLAŞIK KOT : 65 m

GÖZLEM SÜRESİ : 01.10.1988 - 30.09.2006

ORTALAMA AKIMLAR : Gözlem süresinde 19.522 m3/sn. (14 Yıllık) 2006 Su yılında ---- m3/sn.

ANLIK EN ÇOK VE EN AZ AKIMLAR:

2006 Su yılında anlık ençok akım : ----- m3/sn

2006 Su yılında anlık enaz akım : ----- m3/sn

Gözlem süresinde anlık ençok akım : 530. m3/sn 10.04.1991

Gözlem süresinde anlık enaz akım : 4.58 m3/sn 03.07.2001

İstasyon için kullanılmış anahtar bulunamadı.

Akımlar 01 Ekim 2005 'den 30 Eylül 2006' a kadar m3/sn olarak

Gün	Ekim	Kasım	Aralık	Ocak	Şubat	Mart	Nisan	Mayıs	Haziran	Temmuz	Ağustos	Eylül
01	8.50	10.0	-----	19.0	15.7	39.5	32.3	-----	9.50	8.35	7.50	6.50
02	8.50	-----	-----	16.8	15.7	36.8	30.5	-----	11.0	7.85	7.50	6.80
03	8.50	-----	-----	15.7	-----	35.9	28.7	-----	10.0	8.20	7.50	6.80
04	9.00	-----	-----	15.2	-----	-----	27.8	-----	9.50	9.00	7.50	7.15
05	-----	-----	-----	-----	-----	-----	26.9	-----	9.00	9.50	7.15	6.80
06	-----	-----	-----	-----	-----	-----	26.9	-----	8.50	9.50	6.80	6.80
07	-----	-----	11.5	-----	-----	-----	26.0	-----	8.50	9.50	6.80	6.80
08	-----	-----	11.5	-----	-----	-----	26.0	-----	8.50	9.00	6.80	6.80
09	-----	-----	11.5	-----	-----	-----	26.9	-----	10.0	9.00	6.80	6.80
10	-----	-----	11.5	-----	-----	-----	25.3	-----	11.0	8.50	6.80	6.80
11	-----	-----	11.0	-----	67.4	-----	25.3	-----	10.0	8.50	6.50	6.80
12	-----	-----	11.0	-----	48.0	-----	24.6	-----	11.0	8.50	6.50	6.80
13	-----	-----	11.0	-----	35.9	-----	-----	-----	11.0	8.50	6.50	6.80
14	-----	-----	11.0	-----	29.6	-----	-----	-----	11.0	8.50	6.50	7.15
15	-----	-----	11.0	-----	27.8	-----	-----	-----	10.5	8.50	6.50	6.80
16	-----	-----	11.0	-----	26.0	-----	-----	-----	11.0	8.50	6.20	6.80
17	-----	-----	12.5	-----	25.3	-----	-----	-----	10.5	8.50	6.20	7.15
18	-----	-----	12.0	-----	35.9	-----	-----	-----	10.5	8.50	6.20	7.15
19	-----	-----	13.5	-----	40.4	-----	-----	-----	10.0	8.50	6.20	7.50
20	-----	-----	14.1	-----	42.2	-----	-----	-----	9.50	8.35	6.20	7.50
21	-----	-----	13.5	-----	41.3	-----	-----	-----	9.00	8.20	6.20	7.85
22	-----	-----	13.0	-----	39.5	-----	-----	-----	8.50	8.20	6.20	7.85
23	-----	-----	13.0	-----	37.7	-----	-----	12.5	8.50	8.20	6.20	8.50
24	-----	-----	13.0	-----	36.8	-----	-----	12.0	8.35	8.20	5.90	8.35
25	-----	-----	12.5	-----	36.8	-----	-----	11.5	8.20	8.20	5.90	8.50
26	-----	-----	12.5	-----	41.3	-----	-----	11.0	8.20	8.20	6.20	9.00
27	-----	-----	14.1	-----	46.0	-----	-----	11.0	8.20	7.85	6.20	9.00
28	-----	-----	19.0	-----	44.0	-----	-----	10.5	7.85	7.85	6.20	8.50
29	-----	-----	17.9	-----	-----	35.0	-----	10.5	8.20	7.85	6.20	9.50
30	-----	-----	16.3	-----	-----	35.0	-----	10.0	8.35	7.50	6.20	10.5
31	-----	-----	16.8	-----	-----	35.0	-----	10.0	-----	7.50	6.20	-----
Maks.	--	--	--	--	--	--	--	--	16.8	10.0	7.85	10.5
Min.	--	--	--	--	--	--	--	--	7.85	7.50	5.90	6.50
Ortalama	--	--	--	--	--	--	--	--	9.46	8.42	6.52	7.53
LT/SN/Km2	--	--	--	--	--	--	--	--	2.06	1.83	1.42	1.64
AKIM mm.	--	--	--	--	--	--	--	--	5.34	4.91	3.81	4.25
MİL. M3	--	--	--	--	--	--	--	--	24.5	22.6	17.5	19.5

SU YILI (2006)

03. Susurluk Havzasi

D03A090 Orhaneli Ç Deliballilar

YERİ : **BURSA-ORHANELİ yolu üzerinde Orhaneli karayolu köprüsünegelmeden önce sola Deliballılar köyü istikametine dönülür.**
28°59'11" Doğu - 29°55'52" Kuzey

YAĞIŞ ALANI : 3505,60 km2 **YAKLAŞIK KOT :** 350 m

GÖZLEM SÜRESİ : **22.06.1990 - 30.09.2006**

ORTALAMA AKIMLAR : Gözlem süresinde 12.546 m3/sn. (17 Yıllık) 2006 Su yılında 14.471 m3/sn.

ANLIK EN ÇOK VE EN AZ AKIMLAR:

2006 Su yılında anlık ençok akım	:	**79.6**	**m3/sn**	**01.03.2006**
2006 Su yılında anlık enaz akım	:	**2.99**	**m3/sn**	**27.08.2006**
Gözlem süresinde anlık ençok akım	:	**162.**	**m3/sn**	**26.12.2001**
Gözlem süresinde anlık enaz akım	:	**2.08**	**m3/sn**	**20.08.1994**

İstasyon için kullanılmış anahtar bulunamadı.

Akımlar 01 Ekim 2005 'den 30 Eylül 2006' a kadar m3/sn olarak

Gün	Ekim	Kasım	Aralık	Ocak	Şubat	Mart	Nisan	Mayıs	Haziran	Temmuz	Ağustos	Eylül
01	6.83	8.03	10.6	20.7	10.9	50.9	29.3	18.3	9.02	6.59	5.47	2.99
02	7.55	8.03	10.1	16.6	11.1	49.7	26.9	18.6	10.6	6.59	5.25	3.18
03	8.51	8.03	9.55	14.7	11.1	57.8	26.2	18.3	9.28	6.35	5.25	3.38
04	8.27	8.03	9.28	14.1	11.1	72.7	25.8	17.9	9.28	6.35	5.25	3.57
05	7.79	8.03	9.02	13.5	11.1	56.8	25.5	17.6	9.28	6.35	5.25	3.76
06	7.79	8.51	8.75	13.5	12.6	50.1	25.1	17.3	9.28	6.35	5.03	3.96
07	7.55	9.02	8.51	13.5	13.5	47.6	24.8	17.0	9.02	6.35	5.03	4.15
08	7.55	9.02	8.51	13.2	12.9	47.6	24.8	16.6	9.02	6.35	5.03	4.37
09	7.55	8.51	8.75	12.6	12.6	48.0	24.8	16.3	9.02	6.35	5.03	4.59
10	7.55	8.27	8.75	12.3	13.8	45.1	24.4	16.0	9.02	6.35	5.03	5.25
11	7.55	8.27	8.51	12.0	37.6	43.4	24.4	15.7	8.75	6.35	4.81	5.47
12	7.55	8.03	8.27	11.4	35.1	59.2	24.1	15.4	8.75	6.35	4.81	5.69
13	7.79	8.03	8.27	11.1	25.1	51.8	24.8	15.0	8.75	6.13	4.81	5.91
14	7.79	8.03	8.27	10.9	22.7	50.5	24.8	14.7	8.51	6.13	4.59	6.13
15	7.79	7.79	8.03	10.9	25.1	48.4	24.1	14.4	8.27	6.13	4.59	6.35
16	7.79	8.27	8.75	10.6	25.1	45.1	23.4	14.4	8.03	6.13	4.15	6.35
17	7.79	8.03	10.1	10.3	25.8	43.8	22.4	13.8	8.03	6.13	3.76	6.59
18	7.79	8.51	9.81	10.3	27.6	41.8	22.0	13.2	8.03	6.13	3.38	6.59
19	9.02	9.28	14.4	11.4	32.6	41.3	21.3	12.9	8.03	6.13	3.38	6.83
20	8.27	10.3	14.4	14.1	38.8	40.1	20.7	12.6	8.03	6.13	3.38	6.83
21	8.27	10.9	12.6	12.3	45.1	38.0	20.3	12.3	8.03	5.91	3.38	6.83
22	8.03	9.55	11.7	11.4	46.8	36.8	20.0	11.7	7.79	5.91	3.38	7.07
23	8.03	9.02	11.4	11.7	47.6	36.3	20.0	11.4	7.79	5.91	3.18	7.07
24	8.03	8.75	11.1	11.1	48.4	34.7	19.6	11.1	7.79	5.91	3.18	7.07
25	7.79	9.55	10.9	11.1	49.7	35.1	19.0	10.9	7.79	5.91	3.18	7.07
26	7.79	15.0	10.9	11.1	54.4	34.3	18.6	10.6	6.59	5.91	3.18	7.31
27	7.79	14.7	10.9	10.9	60.2	33.4	18.3	10.3	6.59	5.91	2.99	7.07
28	7.79	13.8	11.1	10.9	57.3	32.6	18.3	10.1	6.59	5.91	2.99	7.07
29	7.79	12.3	13.2	10.6	-----	32.2	18.3	9.81	6.59	5.69	2.99	7.31
30	7.79	11.4	14.1	10.6	-----	32.6	18.3	9.55	6.59	5.69	2.99	9.28
31	8.03	-----	17.3	10.9	-----	32.2	-----	9.28	-----	5.47	2.99	-----
Maks.	10.6	16.0	22.4	22.7	65.0	79.6	30.1	18.6	12.9	6.59	5.47	9.28
Min.	6.83	7.55	7.79	9.81	10.3	29.3	18.3	9.28	6.59	5.47	2.99	2.99
Ortalama	7.85	9.43	10.5	12.3	29.5	44.2	22.7	14.0	8.27	6.12	4.12	5.84
LT/SN/Km2	2.24	2.69	3.00	3.50	8.41	12.6	6.47	3.98	2.36	1.75	1.18	1.66
AKIM mm.	5.99	6.97	8.03	9.37	20.4	33.8	16.8	10.7	6.12	4.68	3.15	4.32
MİL. M3	21.0	24.5	28.2	32.9	71.3	118.	58.8	37.4	21.4	16.4	11.0	15.1

SU YILI (2006) YILLIK TOPLAM AKIM 456.00 MİLYON M3 130 MM. 4.1 LT/SN/Km2

03. Susurluk Havzasi

D03A095 KABAKLAR D. HASANLAR

YERİ : KÜTAHYA HİSARCIK İLÇESİNDEN 5 KM SOSE YOL İLE HASANLAR KÖYÜNE ORADAN 5 KM. KABAKLAR KÖYÜ YÖNÜNDE YOLUN SOLUNDADIR
29°7'0" Doğu - 39°15'0" Kuzey

YAĞIŞ ALANI : 43.80 km2 **YAKLAŞIK KOT** : 875 m

GÖZLEM SÜRESİ : 01.10.1990 - 30.09.2006

ORTALAMA AKIMLAR : Gözlem süresinde 0.247 m3/sn. (14 Yıllık) 2006 Su yılında 0.277 m3/sn.

ANLIK EN ÇOK VE EN AZ AKIMLAR:

2006 Su yılında anlık ençok akım	:	2.11	m3/sn	11.02.2006
2006 Su yılında anlık enaz akım	:	0.000	m3/sn	01.10.2005
Gözlem süresinde anlık ençok akım	:	10.1	m3/sn	07.08.1994
Gözlem süresinde anlık enaz akım	:	0.000	m3/sn	04.10.1997

Akımlar 01 Ekim 2005 'den 30 Eylül 2006' a kadar m3/sn olarak

Gün	Ekim	Kasım	Aralık	Ocak	Şubat	Mart	Nisan	Mayıs	Haziran	Temmuz	Ağustos	Eylül
01	KURU	0.012	1.05	0.238	0.304	1.38	0.840	0.238	0.037	0.012	KURU	0.012
02	KURU	0.012	1.05	0.238	0.238	1.38	0.739	0.238	0.037	0.012	KURU	0.012
03	KURU	KURU	0.941	0.238	0.238	1.97	0.739	0.238	0.037	0.012	KURU	0.012
04	KURU	KURU	1.05	0.176	0.238	1.73	0.739	0.238	0.037	0.012	KURU	0.012
05	KURU	0.012	0.941	0.176	0.238	1.38	0.643	0.238	0.037	KURU	KURU	0.012
06	KURU	0.012	1.05	0.238	0.304	1.27	0.546	0.238	0.037	KURU	0.012	0.012
07	KURU	KURU	1.05	0.238	0.464	1.27	0.546	0.238	0.037	KURU	0.012	0.012
08	KURU	KURU	0.941	0.238	0.464	1.38	0.546	0.304	0.037	KURU	0.012	0.012
09	KURU	KURU	1.05	0.238	0.379	1.38	0.546	0.238	0.037	0.012	0.012	0.012
10	KURU	KURU	1.05	0.238	0.379	1.27	0.464	0.238	0.037	0.012	0.012	0.012
11	KURU	KURU	0.941	0.238	1.62	1.05	0.464	0.238	0.037	0.012	0.012	0.012
12	KURU	KURU	1.05	0.176	1.38	1.27	0.379	0.238	0.037	KURU	0.012	0.012
13	KURU	KURU	0.464	0.125	0.941	1.38	0.379	0.238	0.037	0.012	0.012	KURU
14	KURU	KURU	0.037	0.125	0.643	1.38	0.379	0.238	0.037	0.012	0.012	KURU
15	KURU	KURU	0.037	0.125	0.546	1.38	0.379	0.176	0.037	0.012	0.012	KURU
16	KURU	KURU	0.037	0.125	0.546	1.38	0.379	0.176	0.037	0.012	KURU	KURU
17	KURU	KURU	0.125	0.125	0.464	1.27	0.304	0.176	0.037	0.012	0.012	KURU
18	KURU	KURU	0.176	0.125	0.464	1.27	0.304	0.176	0.037	0.012	0.012	KURU
19	KURU	KURU	0.739	0.176	0.643	1.15	0.304	0.176	0.012	0.012	0.012	KURU
20	KURU	KURU	0.464	0.304	0.643	1.05	0.304	0.125	0.012	0.012	0.012	KURU
21	KURU	0.012	0.379	0.238	0.840	0.941	0.304	0.125	0.012	0.012	0.012	KURU
22	KURU	0.012	0.304	0.238	0.840	0.941	0.304	0.125	0.012	KURU	0.012	KURU
23	KURU	KURU	0.238	0.238	0.840	0.941	0.304	0.125	0.012	KURU	0.012	KURU
24	KURU	KURU	0.176	0.176	0.941	1.05	0.238	0.125	0.012	KURU	0.012	KURU
25	KURU	0.012	0.176	0.125	0.941	1.05	0.238	0.125	0.012	KURU	0.012	KURU
26	KURU	0.304	0.125	0.125	1.15	1.05	0.238	0.125	0.012	KURU	0.012	KURU
27	KURU	0.238	0.125	0.176	1.38	0.941	0.238	0.125	0.012	KURU	0.012	KURU
28	KURU	0.176	0.125	0.176	1.38	0.840	0.238	0.125	0.012	KURU	0.012	KURU
29	KURU	0.464	0.125	0.238	-----	0.840	0.238	0.077	0.012	KURU	0.012	KURU
30	KURU	1.15	0.176	0.238	-----	0.840	0.238	0.077	0.012	KURU	0.012	KURU
31	KURU	-----	0.176	0.238	-----	0.941	-----	0.077	-----	KURU	0.012	-----
Maks.	KURU	1.15	1.05	0.304	2.11	1.97	0.941	0.379	0.077	0.012	0.012	0.012
Min.	KURU	KURU	0.012	0.125	0.238	0.464	0.238	0.012	KURU	KURU	KURU	KURU
Ortalama	KURU	0.081	0.528	0.197	0.695	1.21	0.417	0.182	0.027	0.006	0.010	0.005
LT/SN/Km2	0.000	1.84	12.1	4.50	15.9	27.5	9.51	4.15	0.616	0.141	0.221	0.110
AKIM mm.	0.000	4.77	32.3	12.0	38.4	73.7	24.7	11.1	1.60	0.379	0.592	0.284
MİL. M3	0.000	0.209	1.41	0.528	1.68	3.23	1.08	0.487	0.070	0.017	0.026	0.012

SU YILI (2006) YILLIK TOPLAM AKIM 8.75 MİLYON M3 200 MM. 6.3 LT/SN/Km2

03. Susurluk Havzasi

D03A096 OBEN DERESİ OKÇULAR

YERİ : BİGADIÇ- YAĞCILAR KÖYÜNÜN 26. KM SINDEKI KÖPRÜNÜN 50 M MEMBAINDADIR
28°18'27" Doğu - 39°24'33" Kuzey

YAĞIŞ ALANI : 24.70 km2 YAKLAŞIK KOT : 405 m

GÖZLEM SÜRESİ : 01.10.1990 - 30.09.2006

ORTALAMA AKIMLAR : Gözlem süresinde 0.265 m3/sn. (16 Yıllık) 2006 Su yılında 0.308 m3/sn.

ANLIK EN ÇOK VE EN AZ AKIMLAR:

2006 Su yılında anlık ençok akım	:	31.2	m3/sn	11.03.2006
2006 Su yılında anlık enaz akım	:	0.000	m3/sn	21.07.2006
Gözlem süresinde anlık ençok akım	:	31.2	m3/sn	11.03.2006
Gözlem süresinde anlık enaz akım	:	0.000	m3/sn	26.06.1994

89. Anahtar Eğrisi (Seviyeler cm olarak)

Seviye	Akım	Seviye	Akım	Seviye	Akım	Seviye	Akım
50	0.000	65	0.310	94	2.7	140	9.4
53	0.003	68	0.425	100	3.5	150	11.0
55	0.024	72	0.620	110	4.8	152	11.4
57	0.060	82	1.4	120	6.3	160	12.7
60	0.123	90	2.2	130	7.8	260	25.0

Akımlar 01 Ekim 2005 'den 30 Eylül 2006' a kadar m3/sn olarak

Gün	Ekim	Kasım	Aralık	Ocak	Şubat	Mart	Nisan	Mayıs	Haziran	Temmuz	Ağustos	Eylül
01	0.082	0.024	0.162	0.972	0.237	1.06	0.340	0.162	0.040	0.024	0.003	0.001
02	0.162	0.024	0.123	0.523	0.237	0.884	0.310	0.162	0.040	0.024	0.003	0.001
03	0.024	0.024	0.103	0.340	0.237	1.24	0.310	0.162	0.040	0.010	0.003	0.002
04	0.024	0.040	0.103	0.273	0.237	1.06	0.310	0.123	0.040	0.010	0.003	0.002
05	0.024	0.040	0.082	0.237	0.237	0.796	0.310	0.123	0.024	0.024	0.010	0.002
06	0.024	0.040	0.082	0.237	2.58	0.620	0.273	0.123	0.024	0.010	0.003	0.002
07	0.024	0.040	0.082	0.200	1.32	1.06	0.273	0.162	0.024	0.010	0.002	0.002
08	0.024	0.040	0.082	0.200	0.796	1.98	0.237	0.123	0.024	0.010	0.001	0.001
09	0.024	0.040	0.123	0.162	0.796	1.32	0.237	0.123	0.060	0.024	0.002	0.001
10	0.024	0.040	0.103	0.162	4.20	1.06	0.237	0.123	0.060	0.010	0.003	0.001
11	0.024	0.040	0.082	0.123	5.28	2.85	0.200	0.123	0.060	0.010	0.002	0.002
12	0.024	0.040	0.082	0.123	2.58	6.00	0.200	0.123	0.060	0.024	0.002	0.003
13	0.024	0.060	0.082	0.123	1.62	2.46	0.200	0.162	0.060	0.010	KURU	0.002
14	0.024	0.040	0.082	0.103	1.15	2.34	0.237	0.123	0.060	0.024	0.001	0.002
15	0.024	0.040	0.082	0.103	0.884	1.74	0.200	0.123	0.060	0.010	0.002	0.002
16	0.024	0.040	0.200	0.103	0.620	1.41	0.200	0.123	0.060	0.010	0.002	0.002
17	0.024	0.060	0.310	0.103	0.620	1.15	0.200	0.123	0.060	0.010	0.001	0.003
18	0.024	0.200	0.310	0.082	1.50	1.06	0.200	0.103	0.040	0.003	0.002	0.003
19	0.024	0.082	0.972	0.340	1.50	0.972	0.200	0.082	0.024	0.010	KURU	0.003
20	0.024	0.340	0.523	0.708	1.50	0.796	0.200	0.082	0.024	0.003	0.001	0.003
21	0.024	0.162	0.340	0.383	1.32	0.708	0.200	0.082	0.024	0.002	0.001	0.010
22	0.024	0.103	0.273	0.340	1.24	0.620	0.200	0.082	0.024	0.003	0.001	0.010
23	0.024	0.123	0.237	0.425	1.06	0.523	0.200	0.082	0.024	0.002	0.002	0.024
24	0.024	0.237	0.200	0.340	0.972	0.796	0.162	0.060	0.024	0.003	0.002	0.024
25	0.024	0.796	0.200	0.310	1.62	0.796	0.162	0.060	0.040	0.010	KURU	0.024
26	0.024	1.41	0.200	0.273	1.98	0.708	0.162	0.060	0.024	0.010	KURU	0.024
27	0.024	0.972	0.340	0.237	1.50	0.523	0.162	0.060	0.024	0.003	0.001	0.024
28	0.024	0.340	0.383	0.237	1.24	0.425	0.162	0.060	0.024	0.003	KURU	0.024
29	0.024	0.273	0.708	0.162	-----	0.383	0.162	0.060	0.024	0.010	KURU	0.123
30	0.040	0.200	0.425	0.123	-----	0.383	0.162	0.060	0.024	0.003	0.002	0.060
31	0.024	-----	1.24	0.200	-----	0.340	-----	0.040	-----	0.003	0.002	-----
Maks.	0.310	5.28	2.70	4.05	6.40	31.2	0.383	0.200	0.103	0.060	0.010	0.383
Min.	0.010	0.024	0.060	0.082	0.200	0.340	0.162	0.040	0.010	KURU	KURU	KURU
Ortalama	0.031	0.197	0.268	0.266	1.40	1.23	0.220	0.105	0.038	0.010	0.002	0.013
LT/SN/Km2	1.25	7.98	10.9	10.8	56.5	49.7	8.92	4.26	1.54	0.421	0.074	0.522
AKIM mm.	3.34	20.7	29.1	28.8	137.	133.	23.1	11.4	3.99	1.13	0.199	1.35
MİL. M3	0.083	0.511	0.719	0.713	3.38	3.29	0.571	0.282	0.098	0.028	0.005	0.033

SU YILI (2006) YILLIK TOPLAM AKIM 9.71 MİLYON M3 393 MM. 12.5 LT/SN/Km2

03. Susurluk Havzasi

D03A102 Orhaneli Ç. Çayören

YERİ : BURSA KELES İLÇESİNDEN TUNÇ BİLEK YOLUNA SAPILIRDENİZLER KÖ-
29°49'48" Doğu - 39°48'52" Kuzey

YAĞIŞ ALANI : 2830,80 km2 YAKLAŞIK KOT : 575 m

GÖZLEM SÜRESİ : 02.06.1994 - 30.09.2006

ORTALAMA AKIMLAR : Gözlem süresinde 11.337 m3/sn. (11 Yıllık) 2006 Su yılında 10.703 m3/sn.

ANLIK EN ÇOK VE EN AZ AKIMLAR:

2006 Su yılında anlık ençok akım	:	58.9	m3/sn	04.03.2006
2006 Su yılında anlık enaz akım	:	3.64	m3/sn	15.08.2006
Gözlem süresinde anlık ençok akım	:	145.	m3/sn	26.12.2001
Gözlem süresinde anlık enaz akım	:	1.70	m3/sn	03.10.1994

İstasyon için kullanılmış anahtar bulunamadı.

Akımlar 01 Ekim 2005 'den 30 Eylül 2006' a kadar m3/sn olarak

Gün	Ekim	Kasım	Aralık	Ocak	Şubat	Mart	Nisan	Mayıs	Haziran	Temmuz	Ağustos	Eylül
01	4.90	5.40	7.60	12.7	6.60	37.2	20.5	12.2	6.46	5.80	4.75	3.88
02	5.23	5.40	7.15	10.7	6.75	37.2	19.2	12.7	6.46	6.65	4.75	4.11
03	6.60	5.60	6.90	9.62	6.75	43.6	18.9	11.6	6.46	6.84	4.64	4.21
04	5.80	5.60	6.75	9.10	6.75	47.3	18.7	10.9	6.27	6.65	4.43	4.32
05	5.40	5.95	6.35	8.58	6.75	39.8	18.7	10.6	6.08	6.46	4.11	4.21
06	5.40	6.35	6.10	8.58	9.36	38.0	18.4	10.6	5.94	6.27	3.98	4.21
07	5.23	7.15	6.10	8.84	9.88	37.2	18.4	11.1	5.94	5.94	3.98	4.11
08	5.23	6.60	5.95	8.58	9.62	37.2	18.4	13.0	6.46	5.67	3.98	4.11
09	5.23	6.10	5.95	8.06	9.88	36.8	18.4	12.7	6.65	5.67	3.88	3.98
10	5.23	5.95	5.95	7.80	10.4	34.8	18.2	11.9	6.84	5.67	3.88	3.98
11	5.23	5.80	5.80	7.60	32.4	34.0	17.9	11.1	8.13	5.53	3.88	3.98
12	5.23	5.60	5.80	7.40	30.4	36.8	17.6	10.9	7.91	5.26	3.88	4.11
13	5.40	5.60	5.60	7.15	23.4	36.4	18.2	10.9	7.25	5.39	3.88	4.32
14	5.23	5.60	5.60	7.15	21.5	35.6	18.2	10.9	7.03	5.80	3.88	4.21
15	5.40	5.80	5.60	7.15	23.4	34.8	17.6	10.6	7.25	5.94	3.76	4.21
16	5.40	5.80	5.60	6.75	23.4	33.6	16.9	10.6	7.25	5.94	3.76	4.11
17	5.40	5.60	5.60	6.75	23.8	32.8	16.2	10.4	7.47	5.94	3.76	4.11
18	6.10	6.75	5.95	6.75	24.8	31.6	15.8	10.1	7.03	5.39	3.76	4.11
19	6.10	6.35	6.10	7.15	28.1	32.0	14.8	10.1	6.84	5.13	3.98	4.32
20	5.95	8.06	6.10	8.58	30.8	30.8	14.4	9.91	6.27	5.01	3.98	4.53
21	5.80	7.40	6.10	7.40	37.6	29.5	14.1	9.66	6.08	5.01	3.88	4.88
22	5.60	6.35	6.10	7.15	38.7	29.1	13.8	9.42	5.94	5.01	3.76	4.88
23	5.60	6.10	6.10	6.90	38.7	27.6	14.1	8.55	5.67	5.13	3.76	5.01
24	5.40	5.95	6.10	6.75	37.6	27.2	13.6	8.13	5.53	5.13	3.64	5.39
25	5.40	7.15	6.10	6.75	38.0	27.2	13.0	7.69	5.53	5.26	3.76	6.08
26	5.40	11.4	6.10	6.75	40.5	25.7	12.7	7.47	5.39	5.13	3.64	5.80
27	5.40	12.0	6.10	6.75	40.8	25.3	12.4	7.47	5.39	5.13	3.64	5.39
28	5.40	10.1	6.10	6.75	39.1	24.8	12.2	7.25	5.67	5.01	3.64	5.26
29	5.40	8.84	7.15	6.75	-----	24.8	11.9	7.03	6.65	4.88	3.76	6.46
30	5.40	8.06	8.32	6.60	-----	25.3	11.9	6.84	6.27	4.88	3.76	6.27
31	5.60	-----	11.4	6.60	-----	22.9	-----	6.65	-----	4.88	3.76	-----
Maks.	8.84	12.5	16.4	15.6	42.2	58.9	22.4	13.3	8.76	19.2	4.75	7.69
Min.	4.90	5.40	5.40	6.35	6.60	21.0	11.9	6.65	5.39	4.88	3.64	3.88
Ortalama	5.49	6.81	6.39	7.75	23.4	32.8	16.2	9.97	6.47	5.56	3.93	4.62
LT/SN/Km2	1.94	2.41	2.26	2.74	8.27	11.6	5.71	3.52	2.29	1.96	1.39	1.63
AKIM mm.	5.19	6.24	6.05	7.33	20.0	31.0	14.8	9.43	5.92	5.26	3.72	4.23
MİL. M3	14.7	17.7	17.1	20.7	56.7	87.9	41.9	26.7	16.8	14.9	10.5	12.0

SU YILI (2006) YILLIK TOPLAM AKIM 337.60 MİLYON M3 119 MM. 3.8 LT/SN/Km2

03. Susurluk Havzasi

D03A104 DEĞİRMENDERE DOĞANLAR

YERİ : TAVŞANLI KAZASINDAN ŞAPCI,ÇAMALAN,KARGILI,ÇALTILI LÖYLERİ İSTİKAMETİNDEN DOĞANLAR KÖYÜNE GİDİLİR.KÖYÜN 1 KM DOĞUSUNDA YOLUN SAĞ TARAFINDADIR
29°10'0" Doğu - 39°31'0" Kuzey

YAĞIŞ ALANI : 275.00 km2 YAKLAŞIK KOT : 535 m

GÖZLEM SÜRESİ : 16.08.1994 - 30.09.2006

ORTALAMA AKIMLAR : Gözlem süresinde 0.643 m3/sn. (10 Yıllık) 2006 Su yılında 0.064 m3/sn.

ANLIK EN ÇOK VE EN AZ AKIMLAR:

2006 Su yılında anlık ençok akım	:	0.220	m3/sn	12.02.2006
2006 Su yılında anlık enaz akım	:	0.000	m3/sn	13.06.2006
Gözlem süresinde anlık ençok akım	:	2.86	m3/sn	17.12.2001
Gözlem süresinde anlık enaz akım	:	0.000	m3/sn	11.10.2001

Akımlar 01 Ekim 2005 'den 30 Eylül 2006' a kadar m3/sn olarak

Gün	Ekim	Kasım	Aralık	Ocak	Şubat	Mart	Nisan	Mayıs	Haziran	Temmuz	Ağustos	Eylül
01	0.014	0.047	0.065	0.065	0.093	0.220	0.120	0.120	0.030	KURU	KURU	KURU
02	0.030	0.047	0.065	0.065	0.093	0.220	0.120	0.120	0.030	KURU	KURU	KURU
03	0.030	0.047	0.065	0.065	0.093	0.220	0.153	0.120	0.030	KURU	KURU	KURU
04	0.030	0.047	0.065	0.065	0.065	0.220	0.153	0.120	0.030	KURU	KURU	KURU
05	0.030	0.047	0.065	0.065	0.065	0.220	0.153	0.120	0.030	KURU	KURU	KURU
06	0.030	0.047	0.047	0.065	0.093	0.187	0.153	0.120	0.030	KURU	KURU	KURU
07	0.030	0.047	0.047	0.065	0.093	0.187	0.153	0.120	0.030	KURU	KURU	KURU
08	0.030	0.047	0.047	0.065	0.093	0.187	0.153	0.120	0.030	KURU	KURU	KURU
09	0.030	0.047	0.047	0.065	0.093	0.187	0.153	0.120	0.030	KURU	KURU	KURU
10	0.030	0.047	0.047	0.065	0.093	0.187	0.120	0.120	0.047	KURU	KURU	KURU
11	0.030	0.047	0.047	0.065	0.153	0.187	0.120	0.065	0.047	KURU	KURU	KURU
12	0.030	0.047	0.047	0.065	0.220	0.153	0.120	0.065	0.047	KURU	KURU	KURU
13	0.030	0.047	0.047	0.065	0.220	0.153	0.120	0.065	0.030	KURU	KURU	KURU
14	0.030	0.047	0.047	0.065	0.187	0.153	0.120	0.065	0.014	KURU	KURU	KURU
15	0.030	0.047	0.047	0.065	0.187	0.153	0.120	0.065	0.014	KURU	KURU	0.004
16	0.030	0.047	0.047	0.065	0.187	0.153	0.120	0.065	0.014	KURU	KURU	0.004
17	0.030	0.047	0.047	0.047	0.187	0.153	0.120	0.065	0.014	KURU	KURU	0.004
18	0.047	0.047	0.047	0.047	0.187	0.153	0.120	0.065	0.014	KURU	KURU	0.004
19	0.047	0.047	0.093	0.065	0.187	0.153	0.120	0.065	0.014	KURU	KURU	0.004
20	0.047	0.047	0.065	0.065	0.220	0.153	0.120	0.065	0.014	KURU	KURU	0.004
21	0.047	0.047	0.065	0.065	0.220	0.153	0.120	0.065	0.014	KURU	KURU	0.004
22	0.047	0.047	0.065	0.065	0.220	0.153	0.120	0.047	0.014	KURU	0.004	0.004
23	0.047	0.047	0.065	0.093	0.220	0.153	0.120	0.047	0.014	KURU	0.004	0.004
24	0.047	0.047	0.065	0.093	0.220	0.153	0.120	0.047	0.014	KURU	0.004	0.004
25	0.047	0.047	0.065	0.093	0.220	0.153	0.120	0.030	0.004	KURU	0.004	0.004
26	0.047	0.047	0.065	0.093	0.220	0.153	0.120	0.030	0.004	KURU	0.004	0.004
27	0.047	0.065	0.065	0.093	0.220	0.153	0.120	0.030	KURU	KURU	0.004	0.004
28	0.047	0.065	0.065	0.093	0.220	0.153	0.120	0.030	KURU	KURU	0.004	0.004
29	0.047	0.065	0.065	0.093	-----	0.153	0.120	0.030	KURU	KURU	0.004	0.004
30	0.047	0.065	0.065	0.093	-----	0.120	0.120	0.030	KURU	KURU	0.004	0.004
31	0.047	-----	0.065	0.093	-----	0.120	-----	0.030	-----	KURU	0.004	-----
Maks.	0.047	0.065	0.093	0.093	0.220	0.220	0.153	0.220	0.047	KURU	0.004	0.004
Min.	0.014	0.047	0.047	0.047	0.065	0.120	0.120	0.014	KURU	KURU	KURU	KURU
Ortalama	0.037	0.049	0.058	0.072	0.163	0.168	0.128	0.073	0.020	KURU	0.001	0.002
LT/SN/Km2	0.135	0.180	0.212	0.262	0.593	0.612	0.464	0.266	0.073	0.000	0.005	0.008
AKIM mm.	0.362	0.466	0.568	0.701	1.44	1.64	1.20	0.712	0.189	0.000	0.013	0.020
MİL. M3	0.100	0.128	0.156	0.193	0.395	0.451	0.331	0.196	0.052	0.000	0.003	0.006

SU YILI (2006) YILLIK TOPLAM AKIM 2.01 MİLYON M3 7 MM. 0.2 LT/SN/Km2

03. Susurluk Havzasi

D03A115 Karadere Ismetpasa

YERİ : Karacabey-Bandırma yolunun 18.Km. den sola sapılarak Sulta-niye köyüne varılır.
Dere menbağa doğru 5 Km. takip edilerek
28°9'26" Doğu - 40°9'40" Kuzey

YAĞIŞ ALANI : 3478,80 km2 YAKLAŞIK KOT : 15 m

GÖZLEM SÜRESİ : 01.10.1997 - 30.09.2006

ORTALAMA AKIMLAR : Gözlem süresinde 13.420 m3/sn. (3 Yıllık) 2006 Su yılında 16.277 m3/sn.

ANLIK EN ÇOK VE EN AZ AKIMLAR:

2006 Su yılında anlık ençok akım	:	76.4	m3/sn	15.03.2006
2006 Su yılında anlık enaz akım	:	0.793	m3/sn	05.09.2006
Gözlem süresinde anlık ençok akım	:	76.4	m3/sn	15.03.2006
Gözlem süresinde anlık enaz akım	:	0.049	m3/sn	24.10.2003

İstasyon için kullanılmış anahtar bulunamadı.

Akımlar 01 Ekim 2005 'den 30 Eylül 2006' a kadar m3/sn olarak

Gün	Ekim	Kasım	Aralık	Ocak	Şubat	Mart	Nisan	Mayıs	Haziran	Temmuz	Ağustos	Eylül
01	0.981	8.12	9.62	11.3	4.49	52.4	50.8	36.3	19.8	1.70	1.55	1.01
02	0.981	7.78	9.51	11.4	4.66	51.6	50.4	35.5	19.4	1.99	1.46	1.01
03	0.981	7.43	9.74	11.0	4.83	50.0	50.4	34.6	19.0	1.21	1.31	1.01
04	0.981	8.24	9.51	10.6	5.19	49.8	50.0	34.2	18.7	3.30	1.31	1.01
05	0.981	7.78	9.39	10.4	5.63	49.3	50.0	33.4	16.1	3.50	1.21	0.793
06	0.952	8.24	9.04	10.4	7.16	48.5	49.8	33.0	18.4	3.50	1.13	1.09
07	0.952	8.12	8.47	11.4	11.5	48.3	49.5	32.3	14.0	3.50	1.13	1.09
08	0.952	6.53	8.70	12.1	10.4	48.3	49.5	32.0	7.71	2.78	1.09	1.09
09	3.92	6.62	9.51	12.0	10.9	52.0	49.5	31.5	12.3	2.53	1.09	1.09
10	9.39	6.53	9.74	12.1	12.4	55.2	49.3	31.3	10.9	2.22	1.05	1.09
11	9.28	6.17	9.97	12.6	31.5	62.0	49.3	30.9	10.1	2.11	1.05	1.09
12	9.16	7.66	9.86	12.6	52.0	65.0	49.0	30.4	8.93	1.76	1.05	1.09
13	8.70	6.80	9.51	13.0	37.8	66.0	49.0	30.2	10.2	1.76	1.05	1.09
14	8.81	7.16	9.28	13.1	22.3	66.5	48.8	29.7	11.5	1.82	1.05	1.09
15	8.81	6.44	9.16	12.9	14.3	74.0	48.8	27.7	9.22	2.97	1.05	1.09
16	9.74	5.36	9.51	12.4	10.8	75.2	48.5	27.5	9.37	5.99	1.05	1.09
17	9.28	3.00	8.81	11.1	9.08	59.5	47.8	29.4	8.04	5.89	1.05	1.09
18	8.35	4.74	6.44	3.92	11.5	50.8	44.8	28.6	7.58	6.08	1.05	1.09
19	8.47	6.98	15.5	3.37	25.7	50.0	43.8	27.2	7.25	5.13	1.05	1.09
20	8.12	10.6	17.8	6.71	32.3	50.0	43.5	24.3	6.34	4.61	1.05	1.09
21	7.89	11.1	13.5	7.16	28.3	51.6	43.3	25.1	5.23	4.22	1.05	1.09
22	7.78	8.12	11.4	5.01	21.0	53.2	42.8	25.5	4.83	4.14	1.05	1.09
23	7.66	6.62	11.6	4.74	15.2	53.2	41.8	25.7	4.38	3.65	1.05	1.09
24	7.66	7.07	12.1	5.72	12.2	52.8	40.5	25.7	4.14	3.10	1.05	1.09
25	7.43	6.89	11.5	5.10	13.1	52.8	39.5	25.3	3.37	2.78	1.05	1.41
26	7.78	11.1	10.9	4.49	26.3	52.8	39.0	24.5	3.17	2.59	1.05	2.16
27	7.34	12.1	10.8	4.58	29.2	52.8	38.3	25.1	2.84	2.40	1.01	2.16
28	7.25	10.4	10.7	4.74	48.3	52.0	37.8	23.5	2.65	2.16	1.01	2.16
29	7.78	9.97	10.3	4.74	-----	51.6	37.0	21.8	2.40	2.05	1.05	2.22
30	8.47	9.74	10.8	4.58	-----	51.2	36.8	20.7	1.99	2.16	1.01	3.10
31	9.97	-----	10.9	4.49	-----	51.2	-----	19.6	-----	1.82	1.01	-----
Maks.	10.9	13.5	19.7	13.4	54.4	76.4	51.2	37.0	22.0	11.5	2.40	10.4
Min.	0.922	1.93	3.37	3.22	4.49	48.3	36.3	15.8	1.55	1.21	0.981	0.793
Ortalama	6.35	7.78	10.4	8.70	18.5	54.8	45.6	28.5	9.33	3.08	1.10	1.29
LT/SN/Km2	1.82	2.24	3.00	2.50	5.32	15.8	13.1	8.18	2.68	0.885	0.317	0.371
AKIM mm.	4.89	5.80	8.04	6.70	12.9	42.2	34.0	21.9	6.95	2.37	0.850	0.962
MİL. M3	17.0	20.2	28.0	23.3	44.8	147.	118.	76.2	24.2	8.24	2.96	3.35

SU YILI (2006) YILLIK TOPLAM AKIM 513.25 MİLYON M3 148 MM. 4.7 LT/SN/Km2

03. Susurluk Havzasi

D03A117 BAĞLARYANİ D. ARAPŞAH

YERİ : KÜTAHYA'YA BAĞLI HİSARCIK-SİMAV YOLU KAVŞAĞINDAN 1 KM. MESAFEDEDİR.
29°10'0" Doğu - 39°14'0" Kuzey

YAĞIŞ ALANI : 50.04 km2 YAKLAŞIK KOT : 785 m

GÖZLEM SÜRESİ : 01.10.1997 - 30.09.2006

ORTALAMA AKIMLAR : Gözlem süresinde 0.306 m3/sn. (6 Yıllık) 2006 Su yılında 0.340 m3/sn.

ANLIK EN ÇOK VE EN AZ AKIMLAR:

2006 Su yılında anlık ençok akım	:	4.93	m3/sn	11.02.2006
2006 Su yılında anlık enaz akım	:	0.000	m3/sn	01.10.2005
Gözlem süresinde anlık ençok akım	:	17.8	m3/sn	05.01.2004
Gözlem süresinde anlık enaz akım	:	0.000	m3/sn	01.03.2000

Akımlar 01 Ekim 2005 'den 30 Eylül 2006' a kadar m3/sn olarak

Gün	Ekim	Kasım	Aralık	Ocak	Şubat	Mart	Nisan	Mayıs	Haziran	Temmuz	Ağustos	Eylül
01	KURU	KURU	0.004	0.149	0.112	2.07	0.934	0.258	0.052	0.052	KURU	KURU
02	KURU	KURU	0.004	0.112	0.079	1.92	0.934	0.258	0.052	0.032	KURU	KURU
03	KURU	KURU	0.004	0.079	0.079	3.43	0.837	0.258	0.052	0.032	KURU	KURU
04	KURU	KURU	0.004	0.079	0.052	2.83	0.754	0.258	0.052	0.032	KURU	KURU
05	KURU	KURU	0.004	0.079	0.032	2.07	0.754	0.258	0.052	0.052	KURU	KURU
06	KURU	KURU	0.004	0.079	0.112	1.80	0.754	0.258	0.052	0.032	KURU	KURU
07	KURU	KURU	0.004	0.079	0.203	1.68	0.671	0.258	0.052	0.032	KURU	KURU
08	KURU	KURU	0.004	0.079	0.149	2.52	0.671	0.258	0.052	0.032	KURU	KURU
09	KURU	KURU	0.004	0.079	0.149	2.07	0.671	0.258	0.052	0.032	KURU	KURU
10	KURU	KURU	0.004	0.079	0.421	1.68	0.671	0.258	0.052	0.032	KURU	KURU
11	KURU	KURU	0.004	0.079	3.62	1.44	0.671	0.258	0.052	0.032	KURU	KURU
12	KURU	KURU	0.004	0.079	1.92	3.13	0.671	0.258	0.052	0.032	KURU	KURU
13	KURU	KURU	0.009	0.079	1.13	2.83	0.671	0.258	0.052	0.052	KURU	KURU
14	KURU	KURU	0.032	0.079	0.754	3.28	0.671	0.258	0.052	0.052	KURU	KURU
15	KURU	KURU	0.032	0.079	0.671	2.98	0.671	0.258	0.052	0.052	KURU	KURU
16	KURU	KURU	0.032	0.079	0.587	2.52	0.671	0.258	0.016	0.052	KURU	KURU
17	KURU	KURU	0.052	0.079	0.504	2.22	0.671	0.258	0.016	0.052	KURU	KURU
18	KURU	KURU	0.052	0.079	0.587	1.92	0.587	0.258	0.016	0.052	KURU	KURU
19	KURU	0.001	1.22	0.203	0.671	1.68	0.587	0.258	0.016	0.052	KURU	KURU
20	KURU	0.002	0.312	0.258	1.03	1.56	0.587	0.258	0.016	0.032	KURU	KURU
21	KURU	0.004	0.149	0.112	1.13	1.44	0.587	0.258	0.016	0.004	KURU	KURU
22	KURU	0.004	0.112	0.149	1.03	1.44	0.587	0.258	0.032	KURU	KURU	KURU
23	KURU	0.004	0.079	0.258	1.13	1.44	0.587	0.149	0.052	KURU	KURU	KURU
24	KURU	0.004	0.079	1.13	1.03	1.44	0.587	0.052	0.052	KURU	KURU	KURU
25	KURU	0.004	0.079	1.68	1.44	1.44	0.587	0.052	0.052	KURU	KURU	KURU
26	KURU	0.052	0.079	1.13	1.80	1.44	0.367	0.052	0.052	KURU	KURU	KURU
27	KURU	0.009	0.079	0.837	1.92	1.32	0.258	0.052	0.052	KURU	KURU	KURU
28	KURU	0.004	0.079	0.934	1.92	1.22	0.258	0.052	0.052	KURU	KURU	KURU
29	KURU	0.004	0.079	0.837	-----	1.22	0.258	0.052	0.052	KURU	KURU	KURU
30	KURU	0.004	0.079	0.671	-----	1.22	0.258	0.052	0.052	KURU	KURU	KURU
31	KURU	-----	0.112	0.112	-----	1.13	-----	0.052	-----	KURU	KURU	-----
Maks.	KURU	0.052	1.22	1.68	4.93	4.93	1.03	0.258	0.052	0.052	KURU	KURU
Min.	KURU	KURU	0.004	0.079	0.004	1.03	0.258	0.052	0.004	KURU	KURU	KURU
Ortalama	KURU	0.003	0.090	0.317	0.867	1.95	0.615	0.201	0.044	0.027	KURU	KURU
LT/SN/Km2	0.000	0.064	1.80	6.34	17.3	38.9	12.3	4.02	0.882	0.531	0.000	0.000
AKIM mm.	0.000	0.166	4.82	17.0	41.9	104.	31.8	10.8	2.29	1.42	0.000	0.000
MİL. M3	0.000	0.008	0.241	0.850	2.10	5.22	1.59	0.539	0.114	0.071	0.000	0.000

SU YILI (2006) YILLIK TOPLAM AKIM 10.73 MİLYON M3 214 MM. 6.8 LT/SN/Km2

03. Susurluk Havzasi

D03A118 KARAERİK D. DOMUR

YERİ : KÜTAHYA DAN TAVŞANLI-TUNÇBİLEK'DEN DOMANİÇ'E,DOMİNİÇ ÇIKIŞINDAN 3 KM. SONRA DURABEY KÖY ÇIKIŞINDNA ORMAN DEPOSUNUN KARŞISINDAN SAĞA İNİLİR.500 M. SONRA İSTASYONA VARILIR. 29°37'0" Doğu - 39°49'0" Kuzey

YAĞIŞ ALANI : 48.00 km2 YAKLAŞIK KOT : 875 m

GÖZLEM SÜRESİ : 01.10.1997 - 30.09.2006

ORTALAMA AKIMLAR : Gözlem süresinde 1.052 m3/sn. (7 Yıllık) 2006 Su yılında 1.194 m3/sn.

ANLIK EN ÇOK VE EN AZ AKIMLAR:

2006 Su yılında anlık ençok akım	:	10.9	m3/sn	03.03.2006
2006 Su yılında anlık enaz akım	:	0.008	m3/sn	26.10.2005
Gözlem süresinde anlık ençok akım	:	18.5	m3/sn	04.04.2005
Gözlem süresinde anlık enaz akım	:	0.000	m3/sn	15.11.2000

4. Anahtar Eğrisi (Seviyeler cm olarak)

Seviye	Akım	Seviye	Akım	Seviye	Akım	Seviye	Akım
2	0.002	12	0.015	35	0.224	90	5.6
4	0.004	16	0.026	50	1.0	100	7.9
6	0.006	20	0.042	60	2.0	119	12.7
8	0.008	24	0.061	70	2.8	130	15.6
10	0.011	28	0.096	80	4.2	142	19.5

Akımlar 01 Ekim 2005 'den 30 Eylül 2006' a kadar m3/sn olarak

Gün	Ekim	Kasım	Aralık	Ocak	Şubat	Mart	Nisan	Mayıs	Haziran	Temmuz	Ağustos	Eylül
01	0.151	0.309	1.00	2.63	0.606	3.64	3.22	2.55	0.437	0.267	0.133	0.437
02	0.151	0.309	0.944	2.38	0.606	3.78	3.08	2.55	0.394	0.224	0.133	0.550
03	0.151	0.309	0.831	2.29	0.606	6.52	3.08	2.55	0.352	0.224	0.133	0.493
04	0.133	0.437	0.831	2.29	0.606	4.34	3.36	2.55	0.352	0.224	0.133	0.437
05	0.133	1.67	0.775	2.29	0.606	3.92	3.36	2.55	0.352	0.206	0.115	0.188
06	0.133	1.86	0.775	2.38	0.662	3.92	3.22	2.55	0.352	0.206	0.115	0.087
07	0.115	1.95	0.775	2.29	0.606	3.78	3.36	2.55	0.394	0.206	0.115	0.087
08	0.115	1.00	0.775	2.29	0.662	3.78	3.50	2.55	0.352	0.188	0.115	0.087
09	0.115	0.831	0.775	2.21	0.662	3.50	3.50	2.46	0.352	0.188	0.115	0.087
10	0.096	0.775	0.662	2.04	0.775	3.22	3.50	2.46	0.437	0.169	0.096	0.087
11	0.096	0.719	0.550	2.04	2.04	3.22	3.36	2.46	0.437	0.151	0.096	0.087
12	0.096	0.606	0.550	2.04	1.29	4.20	3.36	2.46	0.394	0.151	0.096	0.087
13	0.096	0.550	0.550	2.04	0.944	4.20	3.92	2.46	0.394	0.151	0.096	0.078
14	0.087	0.550	0.550	2.04	0.887	4.20	4.06	2.46	0.493	0.151	0.087	0.078
15	0.087	1.19	0.550	2.04	0.887	3.92	3.64	2.46	0.437	0.151	0.133	0.078
16	0.087	1.67	0.606	1.76	0.775	2.80	3.22	2.46	0.394	0.169	0.394	0.078
17	0.078	1.57	0.719	1.29	0.719	2.12	3.36	1.86	0.352	0.169	0.394	0.078
18	0.078	2.72	0.944	0.719	0.719	2.12	2.94	1.10	0.309	0.151	0.394	0.078
19	0.078	2.12	0.944	0.719	0.887	2.12	2.80	0.944	0.309	0.151	0.394	0.078
20	0.070	2.94	0.831	0.831	0.944	2.12	2.80	0.887	0.267	0.133	0.394	0.078
21	0.070	2.38	0.662	0.831	1.29	2.12	2.80	0.887	0.224	0.133	0.394	0.115
22	0.070	2.04	0.662	0.775	2.12	2.21	2.80	0.831	0.206	0.133	0.394	0.115
23	0.061	2.04	0.719	0.775	2.72	2.46	2.72	0.831	0.224	0.133	0.394	0.115
24	0.061	1.57	0.662	0.606	2.72	2.94	2.72	0.719	0.206	0.133	0.394	0.115
25	0.056	2.04	0.662	0.719	3.64	2.94	2.63	0.662	0.206	0.133	0.394	0.550
26	0.056	2.21	0.606	0.719	4.06	2.72	2.63	0.606	0.206	0.133	0.394	0.169
27	0.206	2.12	0.606	0.775	3.78	2.72	2.63	0.550	0.206	0.133	0.394	0.169
28	0.206	1.57	0.662	0.719	3.36	2.80	2.55	0.493	0.352	0.133	0.394	0.188
29	0.224	1.57	1.48	0.719	-----	2.80	2.55	0.437	0.352	0.133	0.394	0.606
30	0.352	1.29	2.04	0.606	-----	3.08	2.55	0.437	0.309	0.133	0.394	0.206
31	0.352	-----	3.36	0.606	-----	3.36	-----	0.437	-----	0.133	0.394	-----
Maks.	0.394	4.20	5.04	3.22	6.06	10.9	4.20	4.76	0.775	0.309	0.394	2.38
Min.	0.008	0.309	0.550	0.437	0.606	2.12	2.55	0.437	0.133	0.133	0.070	0.070
Ortalama	0.125	1.43	0.873	1.50	1.43	3.28	3.11	1.67	0.335	0.164	0.259	0.190
LT/SN/Km2	2.59	29.8	18.2	31.2	29.9	68.3	64.7	34.8	6.98	3.42	5.39	3.95
AKIM mm.	6.95	77.2	48.7	83.6	72.3	183.	168.	93.2	18.1	9.17	14.4	10.2
MİL. M3	0.334	3.71	2.34	4.01	3.47	8.78	8.05	4.47	0.868	0.440	0.692	0.491

SU YILI (2006) YILLIK TOPLAM AKIM 37.66 MİLYON M3 784 MM. 24.9 LT/SN/Km2

03. Susurluk Havzasi

D03A120 KAYA D. YEŞİLKÖY

YERİ : KÜTÜHYA-TAVŞANLI YOLU ÜZERİNDE DOMANİÇ'E BAĞLI YEŞİLKÖY'DEKİ KÖPRÜNÜN 300 M. MANSABINDADIR

29°30'0" Doğu - 39°47'0" Kuzey

YAĞIŞ ALANI : 46.94 km2 YAKLAŞIK KOT : 810 m

GÖZLEM SÜRESİ : 01.10.1997 - 30.09.2006

ORTALAMA AKIMLAR : Gözlem süresinde 0.656 m3/sn. (9 Yıllık) 2006 Su yılında 0.601 m3/sn.

ANLIK EN ÇOK VE EN AZ AKIMLAR:

2006 Su yılında anlık ençok akım	:	2.50	m3/sn	13.04.2006
2006 Su yılında anlık enaz akım	:	0.000	m3/sn	26.10.2005
Gözlem süresinde anlık ençok akım	:	9.47	m3/sn	21.04.2000
Gözlem süresinde anlık enaz akım	:	0.000	m3/sn	26.10.2005

Akımlar 01 Ekim 2005 'den 30 Eylül 2006' a kadar m3/sn olarak

Gün	Ekim	Kasım	Aralık	Ocak	Şubat	Mart	Nisan	Mayıs	Haziran	Temmuz	Ağustos	Eylül
01	0.130	0.130	0.419	0.817	0.419	1.35	1.73	1.35	0.698	0.483	0.169	0.088
02	0.130	0.130	0.336	0.817	0.419	1.22	1.73	1.35	0.698	0.483	0.169	0.088
03	0.130	0.130	0.336	0.817	0.419	1.35	1.73	1.35	0.698	0.483	0.169	0.088
04	0.130	0.130	0.336	0.579	0.419	1.35	1.73	1.22	0.579	0.483	0.169	0.088
05	0.130	0.130	0.275	0.579	0.419	1.22	1.73	1.22	0.579	0.483	0.169	0.088
06	0.130	0.215	0.275	0.579	0.419	1.22	1.85	1.22	0.579	0.483	0.169	0.130
07	0.130	0.336	0.275	0.579	0.419	1.22	1.85	1.22	0.579	0.483	0.169	0.130
08	0.130	0.275	0.275	0.579	0.419	1.22	1.85	1.22	0.579	0.483	0.169	0.130
09	0.130	0.215	0.275	0.483	0.419	1.11	1.73	1.22	0.579	0.483	0.169	0.130
10	0.130	0.215	0.275	0.483	0.419	1.00	1.73	1.11	0.579	0.483	0.169	0.130
11	0.130	0.215	0.215	0.483	0.817	1.00	1.73	1.11	0.579	0.483	0.169	0.130
12	0.130	0.215	0.215	0.483	0.698	1.11	1.85	1.11	0.579	0.483	0.169	0.130
13	0.130	0.215	0.215	0.483	0.579	1.22	1.85	1.00	0.579	0.483	0.169	0.130
14	0.130	0.215	0.215	0.483	0.579	1.22	1.73	0.909	0.579	0.483	0.130	0.130
15	0.130	0.215	0.215	0.483	0.483	1.11	1.60	1.00	0.483	0.483	0.130	0.130
16	0.130	0.215	0.215	0.419	0.419	1.35	1.73	1.00	0.483	0.419	0.130	0.130
17	0.130	0.215	0.275	0.419	0.419	1.47	1.73	0.909	0.483	0.419	0.130	0.130
18	0.130	0.419	0.579	0.419	0.483	1.47	1.60	1.00	0.483	0.336	0.130	0.130
19	0.130	0.336	0.483	0.419	0.483	1.47	1.60	0.909	0.483	0.169	0.130	0.130
20	0.130	0.698	0.419	0.419	0.698	1.35	1.60	0.909	0.483	0.169	0.130	0.130
21	0.130	0.483	0.419	0.419	0.909	1.35	1.47	0.909	0.483	0.169	0.088	0.130
22	0.130	0.419	0.336	0.419	0.909	1.47	1.73	0.817	0.483	0.169	0.088	0.130
23	0.130	0.419	0.336	0.419	0.909	1.60	1.73	0.817	0.483	0.169	0.088	0.130
24	0.130	0.419	0.336	0.419	0.909	1.73	1.73	0.817	0.483	0.169	0.088	0.130
25	0.130	0.909	0.336	0.419	1.11	1.73	1.60	0.817	0.483	0.169	0.088	0.130
26	0.275	0.909	0.336	0.419	1.35	1.60	1.60	0.817	0.483	0.169	0.088	0.169
27	0.130	0.909	0.336	0.419	1.22	1.60	1.47	0.817	0.483	0.169	0.088	0.169
28	0.130	0.698	0.336	0.419	1.35	1.73	1.47	0.817	0.483	0.169	0.088	0.169
29	0.130	0.579	0.698	0.336	-----	1.73	1.47	0.698	0.483	0.169	0.088	0.215
30	0.130	0.419	0.579	0.336	-----	1.85	1.35	0.698	0.483	0.169	0.088	0.169
31	0.130	-----	0.909	0.419	-----	1.73	-----	0.698	-----	0.169	0.088	-----
Maks.	1.00	1.85	1.47	1.00	1.85	2.20	2.50	1.73	0.698	0.698	0.419	0.419
Min.	KURU	0.130	0.215	0.336	0.275	0.909	1.35	0.698	0.336	KURU	KURU	KURU
Ortalama	0.135	0.368	0.357	0.492	0.661	1.39	1.68	1.00	0.540	0.342	0.131	0.131
LT/SN/Km2	2.87	7.83	7.61	10.5	14.1	29.7	35.7	21.3	11.5	7.30	2.80	2.79
AKIM mm.	7.68	20.3	20.4	28.1	34.1	79.4	92.6	57.2	29.8	19.5	7.50	7.24
MİL. M3	0.361	0.953	0.957	1.32	1.60	3.73	4.35	2.68	1.40	0.917	0.352	0.340

SU YILI (2006) YILLIK TOPLAM AKIM 18.96 MİLYON M3 404 MM. 12.8 LT/SN/Km2

03. Susurluk Havzasi

D03A129 DURSUNBEY ÇAYI AŞAĞIYAĞCILAR

YERİ : DURSUNBEY İLÇESİ,AŞAĞIYAĞCILAR KÖYÜNDEDİR.
28°38'14" Doğu - 39°30'15" Kuzey

YAĞIŞ ALANI : 466.30 km2 YAKLAŞIK KOT : 425 m

GÖZLEM SÜRESİ : 29.09.2000 - 30.09.2006

ORTALAMA AKIMLAR : Gözlem süresinde 3.060 m3/sn. (6 Yıllık) 2006 Su yılında 4.144 m3/sn.

ANLIK EN ÇOK VE EN AZ AKIMLAR:

2006 Su yılında anlık ençok akım	:	90.9	m3/sn	11.02.2006
2006 Su yılında anlık enaz akım	:	0.000	m3/sn	29.08.2006
Gözlem süresinde anlık ençok akım	:	284.	m3/sn	17.12.2001
Gözlem süresinde anlık enaz akım	:	0.000	m3/sn	26.08.2000

6. Anahtar Eğrisi (Seviyeler cm olarak)

Seviye	Akım	Seviye	Akım	Seviye	Akım	Seviye	Akım
10	0.000	20	0.000	50	1.2	150	39.5
12	0.000	22	0.006	70	4.1	200	75.0
14	0.000	24	0.030	90	9.8	300	198.
16	0.000	28	0.080	110	17.5	350	284.
18	0.000	40	0.500	130	27.8	360	302.

Akımlar 01 Ekim 2005 'den 30 Eylül 2006' a kadar m3/sn olarak

Gün	Ekim	Kasım	Aralık	Ocak	Şubat	Mart	Nisan	Mayıs	Haziran	Temmuz	Ağustos	Eylül
01	0.060	0.104	2.42	16.5	4.10	22.7	6.32	1.84	0.610	0.202	0.014	0.010
02	0.060	0.104	2.13	10.2	4.10	19.2	5.76	1.84	0.565	0.202	0.014	0.014
03	0.075	0.118	1.99	7.44	4.10	32.9	5.20	1.70	0.565	0.118	0.014	0.014
04	0.194	0.156	1.84	5.76	4.76	26.9	5.20	1.70	0.475	0.118	0.014	0.014
05	0.156	0.194	1.55	4.76	4.98	18.8	5.48	1.70	0.475	0.118	0.014	0.020
06	0.156	0.233	1.47	5.76	12.0	15.0	4.76	1.55	0.430	0.104	0.010	0.020
07	0.118	0.233	1.38	5.20	16.5	13.1	4.54	1.55	0.430	0.089	0.010	0.020
08	0.118	0.233	1.30	4.76	11.6	17.7	4.54	1.47	0.430	0.089	0.010	0.020
09	0.104	0.233	1.21	4.10	9.28	15.4	4.54	1.47	0.475	0.075	0.010	0.020
10	0.104	0.233	1.21	3.44	12.7	13.1	4.10	1.38	0.520	0.046	0.014	0.020
11	0.089	0.194	1.21	3.00	66.2	13.1	3.88	1.38	0.565	0.046	0.010	0.020
12	0.089	0.194	1.21	2.57	32.4	46.7	3.66	1.30	0.565	0.046	KURU	0.025
13	0.104	0.194	1.21	2.57	20.1	31.2	3.88	2.13	0.520	0.046	KURU	0.025
14	0.118	0.194	1.13	2.28	15.0	25.9	3.88	1.84	0.520	0.046	KURU	0.025
15	0.118	0.194	1.13	2.13	12.0	21.8	3.88	1.70	0.520	0.060	KURU	0.031
16	0.118	0.194	1.04	1.70	9.28	17.3	3.44	1.70	0.475	0.075	KURU	0.031
17	0.118	0.194	1.30	1.84	8.64	14.2	3.00	1.55	0.520	0.060	0.010	0.031
18	0.104	0.580	2.42	1.70	16.5	12.3	2.86	1.47	0.430	0.046	0.010	0.031
19	0.104	1.12	23.6	3.22	21.8	11.6	2.71	1.38	0.385	0.060	0.010	0.025
20	0.104	1.86	10.9	15.4	23.1	9.92	2.71	1.38	0.340	0.031	0.010	0.031
21	0.104	1.86	6.60	8.96	23.1	8.64	2.57	1.30	0.295	0.025	0.010	0.075
22	0.104	1.12	4.54	7.72	21.4	7.72	2.71	1.21	0.250	0.025	KURU	0.075
23	0.104	0.855	3.88	7.44	19.7	8.00	2.86	1.13	0.250	0.025	KURU	0.060
24	0.104	0.920	3.44	6.32	18.4	9.60	2.57	1.04	0.226	0.025	0.010	0.046
25	0.104	2.32	2.71	5.48	26.9	11.2	2.42	1.04	0.202	0.025	KURU	0.060
26	0.104	15.0	2.57	5.20	31.2	12.7	2.28	0.955	0.202	0.025	0.010	0.075
27	0.104	11.6	2.57	4.54	28.4	11.6	2.13	0.955	0.202	0.025	0.010	0.075
28	0.104	7.16	4.32	3.88	23.6	7.44	1.99	0.955	0.178	0.020	KURU	0.075
29	0.104	3.88	7.16	4.10	-----	6.88	1.99	0.785	0.202	0.020	KURU	0.462
30	0.104	2.71	8.00	4.10	-----	6.88	1.99	0.700	0.202	0.020	KURU	0.790
31	0.104	-----	15.8	4.10	-----	7.16	-----	0.655	-----	0.020	KURU	-----
Maks.	0.194	29.5	48.0	23.6	90.9	66.2	6.88	2.57	0.655	0.233	0.014	1.18
Min.	0.046	0.104	1.04	1.21	4.10	6.60	1.99	0.655	0.178	0.010	KURU	KURU
Ortalama	0.108	1.81	3.98	5.36	17.9	16.0	3.59	1.38	0.401	0.062	0.007	0.075
LT/SN/Km2	0.232	3.87	8.53	11.5	38.4	34.4	7.71	2.96	0.860	0.134	0.015	0.160
AKIM mm.	0.622	10.0	22.8	30.8	93.0	92.0	20.0	7.92	2.23	0.358	0.040	0.415
MİL. M3	0.290	4.68	10.6	14.4	43.4	42.9	9.32	3.69	1.04	0.167	0.018	0.194

SU YILI (2006) YILLIK TOPLAM AKIM 130.70 MİLYON M3 280 MM. 8.9 LT/SN/Km2

03. Susurluk Havzasi

D03A130 KİLLİ ÇAYI SARİÇAYIR

YERİ : SARIÇAYIR KÖYÜ İÇINDEKI KÖPRÜNÜN 50 M MENBA TARAFINDADIR.
28°12'5" Doğu - 39°34'53" Kuzey

YAĞIŞ ALANI : 727.00 km2 YAKLAŞIK KOT : 139 m

GÖZLEM SÜRESİ : 01.10.2000 - 30.09.2006

ORTALAMA AKIMLAR : Gözlem süresinde 4.697 m3/sn. (6 Yıllık) 2006 Su yılında 6.422 m3/sn.

ANLIK EN ÇOK VE EN AZ AKIMLAR:

2006 Su yılında anlık ençok akım	:	152.	m3/sn	12.03.2006
2006 Su yılında anlık enaz akım	:	0.000	m3/sn	01.10.2005
Gözlem süresinde anlık ençok akım	:	243.	m3/sn	25.12.2001
Gözlem süresinde anlık enaz akım	:	0.000	m3/sn	13.08.2002

Akımlar 01 Ekim 2005 'den 30 Eylül 2006' a kadar m3/sn olarak

Gün	Ekim	Kasım	Aralık	Ocak	Şubat	Mart	Nisan	Mayıs	Haziran	Temmuz	Ağustos	Eylül
01	KURU	0.368	4.07	24.6	6.60	24.6	12.0	3.90	0.848	0.160	KURU	KURU
02	KURU	0.412	3.50	14.9	7.00	22.6	10.9	3.77	0.770	0.188	KURU	KURU
03	KURU	0.412	3.09	11.7	7.20	41.0	10.3	3.63	0.716	0.160	KURU	KURU
04	0.025	0.500	2.05	9.58	7.40	38.0	10.1	3.36	0.608	0.160	KURU	KURU
05	0.037	0.500	1.95	8.48	7.60	25.4	10.6	3.23	0.456	0.188	KURU	KURU
06	0.018	0.500	1.95	8.70	24.2	20.6	9.58	3.23	0.412	0.160	KURU	KURU
07	0.188	0.456	2.05	8.04	24.6	19.4	9.14	3.23	0.412	0.160	KURU	KURU
08	0.188	0.456	1.95	7.20	16.9	30.0	8.92	3.23	0.456	0.135	KURU	KURU
09	0.188	0.456	2.45	6.60	14.0	25.4	8.92	3.09	0.608	0.110	KURU	KURU
10	0.188	0.456	2.35	5.80	21.0	20.2	8.48	2.96	1.16	0.078	KURU	KURU
11	0.188	0.456	2.05	5.26	99.8	19.0	7.82	2.69	1.08	0.068	KURU	KURU
12	0.248	0.456	1.95	4.75	54.2	94.9	7.40	2.55	1.00	0.037	KURU	KURU
13	0.248	0.456	1.95	4.41	33.0	53.7	7.82	4.07	1.08	0.037	KURU	KURU
14	0.248	0.456	1.85	4.41	23.4	47.5	7.60	3.09	1.08	0.037	KURU	KURU
15	0.248	0.456	1.85	4.07	18.3	40.0	8.04	2.69	0.926	0.037	KURU	KURU
16	0.248	0.456	1.85	4.07	14.9	31.5	7.20	3.23	0.848	0.037	KURU	KURU
17	0.280	0.456	4.92	4.07	13.4	25.8	6.80	2.55	0.770	0.025	KURU	KURU
18	0.280	1.24	4.75	4.07	18.7	23.0	6.40	2.35	0.770	0.018	KURU	KURU
19	0.324	1.85	26.2	4.75	23.4	23.4	6.20	2.25	0.608	0.018	KURU	KURU
20	0.324	4.24	15.9	21.0	22.6	19.0	6.20	2.05	0.554	0.010	KURU	KURU
21	0.324	4.58	10.9	11.2	21.8	17.3	6.00	1.95	0.456	KURU	KURU	0.188
22	0.324	3.77	8.48	9.58	20.6	15.5	5.80	1.85	0.368	KURU	KURU	0.078
23	0.324	3.23	7.20	10.9	19.4	15.5	4.75	1.65	0.368	KURU	KURU	0.037
24	0.324	2.82	6.40	9.58	18.0	17.3	5.09	1.39	0.324	KURU	KURU	0.025
25	0.280	3.77	5.43	8.92	23.4	19.8	4.75	1.39	0.280	KURU	KURU	0.248
26	0.280	19.8	4.92	8.48	41.0	16.6	4.41	1.32	0.248	KURU	KURU	0.160
27	0.280	21.4	5.60	7.82	34.0	15.2	4.07	1.24	0.215	KURU	KURU	0.068
28	0.324	12.2	6.60	7.00	28.5	14.0	3.77	1.24	0.215	KURU	KURU	0.051
29	0.280	7.60	7.60	6.80	-----	13.1	3.90	1.16	0.188	KURU	KURU	1.16
30	0.324	5.60	9.80	6.60	-----	12.8	4.24	1.00	0.188	KURU	KURU	2.15
31	0.324	-----	18.7	6.60	-----	12.8	-----	0.926	-----	KURU	KURU	-----
Maks.	0.368	37.5	43.0	39.5	126.	152.	12.5	7.00	1.39	0.188	KURU	6.80
Min.	KURU	0.368	1.85	3.90	6.40	12.2	3.77	0.848	0.135	KURU	KURU	KURU
Ortalama	0.221	3.33	5.82	8.39	23.7	26.3	7.24	2.46	0.600	0.059	KURU	0.139
LT/SN/Km2	0.304	4.58	8.00	11.5	32.7	36.2	9.96	3.38	0.826	0.081	0.000	0.191
AKIM mm.	0.815	11.9	21.4	30.9	79.0	96.8	25.8	9.06	2.14	0.217	0.000	0.495
MİL. M3	0.592	8.62	15.6	22.5	57.4	70.4	18.8	6.59	1.56	0.158	0.000	0.360

SU YILI (2006) YILLIK TOPLAM AKIM 202.58 MİLYON M3 279 MM. 8.8 LT/SN/Km2

03. Susurluk Havzasi

D03A132 ÇAYLAK DERESİ ÇAYLAK

YERİ : SUSURLUK ÇAYLAK MESİRE YERI IÇINDEDİR.
28°11'12" Doğu - 39°54'7" Kuzey

YAĞIŞ ALANI : 54.70 km2 YAKLAŞIK KOT : 48 m

GÖZLEM SÜRESİ : 01.10.2000 - 30.09.2006

ORTALAMA AKIMLAR : Gözlem süresinde 1.126 m3/sn. (6 Yıllık) 2006 Su yılında 1.169 m3/sn.

ANLIK EN ÇOK VE EN AZ AKIMLAR:

2006 Su yılında anlık ençok akım	:	37.2	m3/sn	11.03.2006
2006 Su yılında anlık enaz akım	:	0.000	m3/sn	24.08.2006
Gözlem süresinde anlık ençok akım	:	65.6	m3/sn	24.12.2001
Gözlem süresinde anlık enaz akım	:	0.000	m3/sn	24.08.2006

Akımlar 01 Ekim 2005 'den 30 Eylül 2006' a kadar m3/sn olarak

Gün	Ekim	Kasım	Aralık	Ocak	Şubat	Mart	Nisan	Mayıs	Haziran	Temmuz	Ağustos	Eylül
01	0.048	0.320	0.320	1.55	1.22	8.32	1.40	0.568	0.150	0.090	0.009	KURU
02	0.235	0.150	0.235	1.22	1.22	6.01	1.40	0.660	0.150	0.090	0.029	0.001
03	0.150	0.150	0.235	0.845	1.22	6.21	1.22	0.568	0.150	0.090	0.009	0.009
04	0.090	0.320	0.235	0.845	1.40	4.82	1.22	0.568	0.150	0.090	0.029	0.005
05	0.090	0.320	0.150	0.660	1.55	3.63	1.22	0.568	0.150	0.090	0.005	0.006
06	0.048	0.235	0.150	0.845	2.18	3.04	1.03	0.568	0.150	0.090	0.003	0.003
07	0.048	0.235	0.150	0.845	2.00	3.24	1.03	0.568	0.150	0.090	0.003	0.004
08	0.048	0.150	0.398	1.40	2.00	4.62	1.03	0.568	0.150	0.048	0.002	0.005
09	0.090	0.150	0.320	1.70	1.70	3.83	1.03	0.568	0.235	0.048	0.002	0.005
10	0.090	0.150	0.150	1.55	4.43	3.44	1.03	0.475	0.235	0.048	0.002	0.005
11	0.090	0.150	0.150	1.40	19.7	9.44	1.03	0.475	0.235	0.048	0.002	0.004
12	0.150	0.150	0.090	1.22	6.80	13.5	1.03	0.475	0.235	0.048	0.002	0.006
13	0.150	0.150	0.090	1.22	4.23	11.9	1.03	0.568	0.235	0.048	0.002	0.006
14	0.090	0.150	0.150	1.03	3.04	7.44	1.03	0.475	0.235	0.090	0.002	0.006
15	0.048	0.150	0.150	1.03	2.53	5.22	1.03	0.475	0.235	0.048	0.002	0.006
16	0.090	0.150	0.320	0.845	2.18	4.23	1.03	0.475	0.235	0.048	0.002	0.006
17	0.090	0.150	0.398	0.845	2.53	3.44	1.03	0.475	0.235	0.048	0.001	0.006
18	0.048	0.150	0.475	0.660	10.2	3.44	1.03	0.398	0.150	0.048	0.002	0.006
19	0.048	0.150	1.22	1.85	11.1	3.04	0.845	0.398	0.150	0.048	0.002	0.006
20	0.048	1.03	0.660	2.70	9.68	2.70	0.845	0.398	0.150	0.048	0.003	0.006
21	0.029	0.475	0.660	1.70	10.2	2.35	0.845	0.398	0.150	0.048	0.003	0.009
22	0.029	0.320	0.568	1.55	10.2	2.18	0.845	0.320	0.150	0.006	0.002	0.029
23	0.029	0.398	0.568	1.70	7.00	2.18	0.660	0.320	0.150	0.005	0.002	0.029
24	0.048	1.55	0.568	1.55	6.41	2.18	0.660	0.320	0.150	0.048	0.001	0.029
25	0.048	2.00	0.568	2.53	10.2	2.00	0.660	0.235	0.150	0.048	0.001	0.090
26	0.090	2.70	0.660	4.03	9.92	2.00	0.660	0.235	0.150	0.048	0.001	0.048
27	0.090	1.22	1.85	1.70	11.1	1.85	0.660	0.235	0.150	0.048	0.001	0.029
28	0.090	0.660	2.35	1.40	7.22	1.85	0.660	0.235	0.150	0.048	0.001	0.090
29	0.090	0.475	1.55	1.22	-----	1.85	0.660	0.235	0.150	0.048	0.001	0.845
30	0.320	0.320	1.03	1.22	-----	1.70	0.660	0.150	0.150	0.029	KURU	0.150
31	0.660	-----	1.70	1.22	-----	1.55	-----	0.150	-----	0.029	KURU	-----
Maks.	3.04	6.21	4.43	6.41	35.2	37.2	3.04	0.845	0.235	0.398	0.029	4.03
Min.	0.029	0.090	0.003	0.660	1.22	1.40	0.660	0.150	0.090	0.004	KURU	KURU
Ortalama	0.107	0.489	0.584	1.42	5.83	4.30	0.950	0.423	0.176	0.055	0.004	0.048
LT/SN/Km2	1.95	8.94	10.7	26.0	107.	78.6	17.4	7.74	3.21	1.00	0.074	0.883
AKIM mm.	5.23	23.2	28.6	69.6	258.	210.	45.0	20.7	8.32	2.69	0.199	2.29
MİL. M3	0.286	1.27	1.57	3.81	14.1	11.5	2.46	1.13	0.455	0.147	0.011	0.125

SU YILI (2006) YILLIK TOPLAM AKIM 36.86 MİLYON M3 674 MM. 21.4 LT/SN/Km2

03. Susurluk Havzasi

D03A133 Narli D. Narlidere Köprü

YERİ : BURSA-ANKARA KARAYOLUNDA 20. KM DEN SOLA DÖNÜLÜR.GÖLBAŞI GÖLÜ NARLIDERE KÖYÜ İÇINDEDIR

29°17'54" Doğu - 40°15'19" Kuzey

YAĞIŞ ALANI : 43,00 km2 YAKLAŞIK KOT : 252 m

GÖZLEM SÜRESİ : 01.10.2000 - 30.09.2005

ORTALAMA AKIMLAR : Gözlem süresinde 0.370 m3/sn. (3 Yıllık) 2005 Su yılında 0.241 m3/sn.

ANLIK EN ÇOK VE EN AZ AKIMLAR:

2005 Su yılında anlık ençok akım	:	29.2	m3/sn	06.03.2005
2005 Su yılında anlık enaz akım	:	0.010	m3/sn	11.08.2005
Gözlem süresinde anlık ençok akım	:	67.6	m3/sn	25.12.2001
Gözlem süresinde anlık enaz akım	:	0.010	m3/sn	11.08.2005

İstasyon için kullanılmış anahtar bulunamadı.

Akımlar 01 Ekim 2004 'den 30 Eylül 2005' a kadar m3/sn olarak

Gün	Ekim	Kasım	Aralık	Ocak	Şubat	Mart	Nisan	Mayıs	Haziran	Temmuz	Ağustos	Eylül
01	0.026	0.042	0.081	0.081	0.220	2.19	0.270	0.640	0.081	0.026	0.026	0.026
02	0.026	0.081	0.081	0.081	0.120	3.55	0.220	0.270	0.081	0.026	0.026	0.026
03	0.026	0.081	0.081	0.081	0.081	2.19	0.220	0.220	0.081	0.026	0.026	0.026
04	0.026	0.081	0.081	0.081	0.120	1.58	0.220	0.220	0.042	0.170	0.026	0.026
05	0.026	0.081	0.081	0.081	0.081	1.11	0.220	0.170	0.042	0.170	0.026	0.026
06	0.026	0.081	0.081	0.081	0.120	5.40	0.220	0.170	0.042	0.042	0.026	0.026
07	0.026	0.081	0.081	0.081	0.120	2.04	0.220	0.170	0.042	0.026	0.026	0.026
08	0.026	0.081	0.081	0.081	0.120	2.04	0.220	0.170	0.042	0.026	0.026	0.026
09	0.026	0.081	0.081	0.081	0.120	1.58	0.220	0.170	0.042	0.026	0.026	0.026
10	0.026	0.081	0.081	0.081	0.170	1.42	0.220	0.170	0.042	0.026	0.026	0.026
11	0.026	0.081	0.081	0.081	0.170	0.960	0.220	0.120	0.042	0.026	0.026	0.026
12	0.026	0.081	0.081	0.081	0.120	0.747	0.220	0.120	0.042	0.026	0.026	0.026
13	0.026	0.081	0.081	0.081	0.220	0.747	0.220	0.120	0.042	0.026	0.026	0.026
14	0.026	0.081	0.081	0.081	2.50	0.640	0.220	0.120	0.042	0.026	0.026	0.042
15	0.026	0.081	0.081	0.081	1.88	0.640	0.170	0.120	0.042	0.026	0.026	0.026
16	0.026	0.081	0.081	0.081	0.853	0.533	0.170	0.081	0.042	0.120	0.026	0.026
17	0.026	0.081	0.081	0.170	0.640	0.533	0.170	0.081	0.042	0.042	0.026	0.026
18	0.026	0.081	0.081	0.081	1.88	0.427	0.170	0.081	0.042	0.042	0.026	0.010
19	0.026	0.081	0.081	0.081	1.58	0.427	0.170	0.081	0.042	0.042	0.026	0.026
20	0.026	0.081	0.081	0.081	1.27	0.427	0.170	0.081	0.042	0.026	0.026	0.026
21	0.026	0.081	0.081	0.081	1.11	0.320	0.170	0.081	0.042	0.026	0.026	0.026
22	0.026	0.081	0.081	0.081	0.640	0.320	0.170	0.081	0.042	0.026	0.026	0.026
23	0.026	0.081	0.081	0.081	0.533	0.320	0.170	0.081	0.042	0.042	0.026	0.026
24	0.026	0.120	0.081	0.081	0.533	0.320	0.170	0.081	0.042	0.042	0.026	0.026
25	0.026	0.081	0.081	0.081	0.533	0.270	0.170	0.081	0.042	0.042	0.026	0.026
26	0.026	0.081	0.081	0.081	0.427	0.270	0.170	0.081	0.042	0.042	0.026	0.026
27	0.026	0.081	0.081	0.081	0.960	0.270	0.170	0.081	0.042	0.026	0.026	0.026
28	0.026	0.081	0.081	2.76	3.81	0.270	0.170	0.081	0.042	0.026	0.026	0.026
29	0.026	0.081	0.081	3.81	-----	0.270	0.170	0.081	0.042	0.026	0.010	0.026
30	0.026	0.081	0.081	4.34	-----	0.270	0.960	0.081	0.026	0.026	0.010	0.026
31	0.026	-----	0.081	0.747	-----	0.270	-----	0.081	-----	0.026	0.026	-----
Maks.	0.026	0.747	0.120	19.6	15.5	29.2	5.00	1.11	0.120	5.76	0.042	0.533
Min.	0.026	0.026	0.081	0.081	0.081	0.220	0.120	0.081	0.026	0.026	0.010	0.010
Ortalama	0.026	0.081	0.081	0.449	0.748	1.04	0.221	0.138	0.045	0.042	0.025	0.026
LT/SN/Km2	0.605	1.88	1.88	10.5	17.4	24.3	5.15	3.20	1.06	0.987	0.581	0.605
AKIM mm.	1.62	4.88	5.05	28.0	42.1	65.0	13.3	8.57	2.73	2.64	1.56	1.57
MİL. M3	0.070	0.210	0.217	1.20	1.81	2.80	0.574	0.369	0.118	0.114	0.067	0.067

SU YILI (2005) YILLIK TOPLAM AKIM 7.62 MİLYON M3 177 MM. 5.6 LT/SN/Km2

03. Susurluk Havzasi

D03A133 Narli D. Narlidere Köprü

YERİ : BURSA-ANKARA KARAYOLUNDA 20. KM DEN SOLA DÖNÜLÜR.GÖLBAŞI GÖLÜ NARLIDERE KÖYÜ İÇINDEDIR
29°17'54" Doğu - 40°15'19" Kuzey

YAĞIŞ ALANI : 43,00 km2 YAKLAŞIK KOT : 252 m

GÖZLEM SÜRESİ : 01.10.2000 - 30.09.2006

ORTALAMA AKIMLAR : Gözlem süresinde 0.432 m3/sn. (4 Yıllık) 2006 Su yılında 0.621 m3/sn.

ANLIK EN ÇOK VE EN AZ AKIMLAR:

2006 Su yılında anlık ençok akım	:	71.2	m3/sn	11.02.2006
2006 Su yılında anlık enaz akım	:	0.026	m3/sn	01.10.2005
Gözlem süresinde anlık ençok akım	:	71.2	m3/sn	11.02.2006
Gözlem süresinde anlık enaz akım	:	0.010	m3/sn	11.08.2005

İstasyon için kullanılmış anahtar bulunamadı.

Akımlar 01 Ekim 2005 'den 30 Eylül 2006' a kadar m3/sn olarak

Gün	Ekim	Kasım	Aralık	Ocak	Şubat	Mart	Nisan	Mayıs	Haziran	Temmuz	Ağustos	Eylül
01	0.026	0.042	0.320	2.04	0.853	2.35	0.820	0.460	0.290	0.128	0.076	0.061
02	0.042	0.042	0.320	1.42	0.853	1.98	0.820	0.460	0.290	0.128	0.076	0.061
03	0.081	0.042	0.747	1.42	0.853	4.44	0.820	0.460	0.290	0.128	0.076	0.061
04	0.081	0.042	0.427	0.960	0.960	2.55	0.720	0.460	0.290	0.128	0.061	0.046
05	0.081	0.042	0.320	0.853	0.960	2.15	0.720	0.460	0.290	0.128	0.061	0.046
06	0.081	0.042	0.320	0.533	0.960	2.15	0.720	0.460	0.290	0.128	0.061	0.046
07	0.081	0.042	0.320	0.320	0.960	2.15	0.620	0.460	0.290	0.128	0.061	0.061
08	0.081	0.042	0.320	0.320	0.960	2.15	0.620	0.460	0.290	0.128	0.061	0.061
09	0.081	0.042	0.320	0.320	0.747	2.15	0.620	0.460	0.290	0.128	0.061	0.061
10	0.081	0.042	0.220	0.320	8.28	2.15	0.620	0.290	0.290	0.128	0.061	0.061
11	0.081	0.042	0.220	0.320	15.5	2.15	0.540	0.290	0.290	0.128	0.061	0.061
12	0.081	0.042	0.220	0.320	2.78	3.00	0.540	0.290	0.290	0.128	0.046	0.046
13	0.081	0.042	0.220	0.320	2.15	2.15	0.540	0.290	0.290	0.128	0.046	0.046
14	0.081	0.042	0.220	0.320	1.80	2.15	0.460	0.290	0.290	0.128	0.046	0.061
15	0.081	0.042	0.220	0.320	1.50	2.15	0.460	0.290	0.290	0.128	0.046	0.061
16	0.081	0.042	0.853	0.320	1.38	2.15	0.375	0.290	0.290	0.128	0.030	0.061
17	0.270	0.042	1.11	0.320	1.38	2.15	0.460	0.290	0.290	0.128	0.046	0.061
18	0.026	0.320	0.747	0.320	1.65	2.15	0.460	0.290	0.290	0.128	0.061	0.061
19	0.026	0.220	1.11	1.73	2.15	2.15	0.460	0.290	0.290	0.076	0.061	0.061
20	0.026	1.58	1.11	1.88	2.15	2.15	0.460	0.290	0.180	0.076	0.076	0.061
21	0.026	0.747	0.747	1.27	2.15	2.15	0.460	0.290	0.128	0.076	0.076	0.061
22	0.026	0.270	0.747	0.853	2.15	1.50	0.460	0.290	0.128	0.076	0.076	0.076
23	0.026	0.270	0.747	0.747	2.15	0.910	0.460	0.290	0.128	0.076	0.076	0.076
24	0.026	0.427	0.747	0.747	2.15	0.820	0.460	0.290	0.128	0.076	0.061	0.076
25	0.026	0.960	0.747	0.747	1.98	0.820	0.460	0.290	0.128	0.076	0.061	0.076
26	0.026	1.42	0.747	0.747	1.80	0.820	0.460	0.290	0.128	0.076	0.061	0.076
27	0.026	1.11	1.11	0.747	3.24	0.820	0.460	0.290	0.128	0.076	0.061	0.076
28	0.026	0.640	2.04	0.747	3.24	0.820	0.460	0.290	0.128	0.076	0.061	0.061
29	0.026	0.747	1.88	0.747	-----	0.820	0.460	0.290	0.128	0.076	0.061	0.620
30	0.026	0.427	1.42	0.747	-----	0.820	0.460	0.290	0.128	0.076	0.061	0.128
31	0.220	-----	3.55	0.747	-----	0.820	-----	0.290	-----	0.076	0.061	-----
Maks.	2.76	7.20	12.0	11.5	71.2	19.0	0.910	0.460	0.375	0.540	0.076	23.8
Min.	0.026	0.042	0.220	0.270	0.533	0.820	0.235	0.290	0.128	0.061	0.030	0.030
Ortalama	0.065	0.328	0.779	0.759	2.42	1.86	0.549	0.339	0.232	0.106	0.061	0.082
LT/SN/Km2	1.52	7.64	18.1	17.6	56.2	43.3	12.8	7.89	5.40	2.47	1.42	1.92
AKIM mm.	4.08	19.8	48.5	47.3	136.	116.	33.1	21.1	14.0	6.61	3.80	4.96
MİL. M3	0.175	0.851	2.09	2.03	5.85	4.98	1.42	0.909	0.602	0.284	0.163	0.213

SU YILI (2006) YILLIK TOPLAM AKIM 19.57 MİLYON M3 455 MM. 14.4 LT/SN/Km2

03. Susurluk Havzasi

D03A135 DOMBAY DERESİ DEDEKAŞI

YERİ : DEDEKAŞI-BİGADIÇ YOLUNUN 3. KM SINDEDIR.
28°9'40" Doğu - 39°35'12" Kuzey

YAĞIŞ ALANI : 238.20 km2 **YAKLAŞIK KOT** : 147 m

GÖZLEM SÜRESİ : 13.11.2000 - 30.09.2006

ORTALAMA AKIMLAR : Gözlem süresinde 1.599 m3/sn. (4 Yıllık) 2006 Su yılında 1.351 m3/sn.

ANLIK EN ÇOK VE EN AZ AKIMLAR:

2006 Su yılında anlık ençok akım	:	71.8	m3/sn	12.03.2006
2006 Su yılında anlık enaz akım	:	0.000	m3/sn	04.06.2006
Gözlem süresinde anlık ençok akım	:	94.2	m3/sn	22.12.2001
Gözlem süresinde anlık enaz akım	:	0.000	m3/sn	04.06.2006

Akımlar 01 Ekim 2005 'den 30 Eylül 2006' a kadar m3/sn olarak

Gün	Ekim	Kasım	Aralık	Ocak	Şubat	Mart	Nisan	Mayıs	Haziran	Temmuz	Ağustos	Eylül
01	0.020	0.027	0.626	4.00	1.20	3.07	1.90	1.08	0.034	0.025	0.007	0.004
02	0.020	0.027	0.552	2.60	1.20	2.60	1.90	1.08	0.020	0.020	0.009	0.007
03	0.027	0.034	0.478	1.67	1.08	4.00	1.90	0.950	0.020	0.029	0.014	0.012
04	0.027	0.034	0.403	1.20	1.20	3.77	1.67	0.950	0.038	0.025	0.014	0.012
05	0.027	0.034	0.329	0.950	1.43	2.60	1.67	0.870	0.056	0.025	0.012	0.012
06	0.027	0.034	0.403	0.950	18.5	1.90	1.67	0.790	0.075	0.029	0.014	0.010
07	0.027	0.034	0.329	0.825	10.9	2.13	1.43	0.695	0.084	0.020	0.014	0.010
08	0.027	0.034	0.255	0.403	5.65	11.7	1.43	0.695	0.104	0.020	0.014	0.007
09	0.027	0.034	0.329	0.626	4.65	6.70	1.43	0.600	0.123	0.016	0.010	0.006
10	0.027	0.034	0.403	0.552	15.9	3.77	1.20	0.541	0.143	0.025	0.012	0.007
11	0.027	0.034	0.329	0.552	35.8	3.77	1.20	0.541	0.104	0.029	0.012	0.010
12	0.027	0.034	0.255	0.478	18.0	35.1	1.20	0.483	0.104	0.056	0.010	0.006
13	0.027	0.034	0.255	0.478	8.13	12.8	1.20	0.870	0.104	0.034	0.003	0.002
14	0.027	0.034	0.255	0.403	4.65	15.4	2.60	0.695	0.104	0.066	0.006	0.001
15	0.041	0.034	0.255	0.403	3.07	10.4	2.37	0.541	0.123	0.029	0.004	0.002
16	0.041	0.034	0.255	0.403	2.37	6.70	1.90	0.424	0.182	0.020	0.003	KURU
17	0.041	0.034	0.950	0.329	2.13	4.98	1.43	0.328	0.182	0.034	0.003	0.002
18	0.034	0.041	0.950	0.329	2.37	4.65	1.20	0.292	0.162	0.016	0.006	0.004
19	0.034	0.056	4.00	0.478	4.00	4.98	1.08	0.255	0.143	0.014	0.006	0.004
20	0.034	0.403	2.83	3.07	4.00	3.30	1.08	0.255	0.056	0.016	0.003	0.010
21	0.034	0.700	1.67	1.90	3.77	2.60	0.950	0.292	0.056	0.014	0.002	0.034
22	0.034	0.403	1.20	1.67	3.30	2.37	0.950	0.219	0.066	0.007	KURU	0.027
23	0.034	0.255	0.825	3.30	2.83	2.13	0.870	0.182	0.066	0.009	0.002	0.020
24	0.034	0.329	0.700	2.37	2.60	2.13	0.870	0.219	0.066	0.010	0.001	0.027
25	0.034	0.825	0.700	1.90	3.53	2.60	0.870	0.084	0.056	0.007	0.002	0.034
26	0.034	6.35	0.700	1.90	7.65	2.13	0.870	0.056	0.056	0.010	0.003	0.027
27	0.034	4.98	0.950	1.67	4.98	1.90	0.790	0.066	0.056	0.010	KURU	0.027
28	0.034	2.37	1.20	1.20	3.77	1.43	0.790	0.066	0.047	0.006	0.002	0.027
29	0.034	1.20	1.67	1.20	-----	1.20	1.43	0.038	0.047	0.016	KURU	0.056
30	0.027	0.950	2.13	1.20	-----	1.08	1.20	0.038	0.047	0.010	KURU	0.110
31	0.027	-----	2.60	1.20	-----	2.13	-----	0.056	-----	0.009	0.002	-----
Maks.	0.041	15.9	6.00	5.65	57.7	71.8	2.60	1.08	0.292	0.066	0.014	0.110
Min.	0.020	0.027	0.227	0.255	1.08	1.08	0.790	0.038	KURU	0.004	KURU	KURU
Ortalama	0.031	0.648	0.929	1.30	6.38	5.36	1.37	0.460	0.084	0.021	0.006	0.017
LT/SN/Km2	0.129	2.72	3.90	5.45	26.8	22.5	5.74	1.93	0.353	0.089	0.026	0.072
AKIM mm.	0.344	7.05	10.4	14.6	64.8	60.2	14.9	5.17	0.916	0.238	0.069	0.188
MİL. M3	0.082	1.68	2.49	3.47	15.4	14.3	3.55	1.23	0.218	0.057	0.016	0.045

SU YILI (2006) YILLIK TOPLAM AKIM 42.54 MİLYON M3 179 MM. 5.7 LT/SN/Km2

03. Susurluk Havzasi

D03A136 KOCAÇAY KAYACA

YERİ : **MANYAS İLÇESI KAYACA KÖYÜ KÖPRÜSÜNÜN 300 M MANSABINDADIR.**
27°58'8" Doğu - 40°4'31" Kuzey

YAĞIŞ ALANI : **2308.80 km2** **YAKLAŞIK KOT : 20.34 m**

GÖZLEM SÜRESİ : **01.11.2002 - 30.09.2006**

ORTALAMA AKIMLAR : **Gözlem süresinde 19.612 m3/sn. (1 Yıllık) 2006 Su yılında 19.612 m3/sn.**

ANLIK EN ÇOK VE EN AZ AKIMLAR:

2006 Su yılında anlık ençok akım	:	**658.**	**m3/sn**	**11.02.2006**
2006 Su yılında anlık enaz akım	:	**0.000**	**m3/sn**	**22.07.2006**
Gözlem süresinde anlık ençok akım	:	**658.**	**m3/sn**	**11.02.2006**
Gözlem süresinde anlık enaz akım	:	**0.000**	**m3/sn**	**22.07.2006**

Akımlar 01 Ekim 2005 'den 30 Eylül 2006' a kadar m3/sn olarak

Gün	Ekim	Kasım	Aralık	Ocak	Şubat	Mart	Nisan	Mayıs	Haziran	Temmuz	Ağustos	Eylül
01	0.900	1.01	8.30	41.7	12.3	108.	17.7	7.74	2.95	1.27	KURU	KURU
02	0.956	0.900	6.46	20.4	14.4	73.2	17.4	7.30	2.95	1.16	KURU	KURU
03	1.01	0.856	5.43	12.2	18.4	53.0	17.1	7.11	2.80	1.04	KURU	KURU
04	1.01	0.812	4.67	9.11	20.9	57.8	16.8	6.91	2.65	0.970	KURU	KURU
05	1.01	0.812	3.98	7.61	21.2	42.0	16.2	6.91	2.50	0.900	KURU	KURU
06	1.01	0.856	3.73	6.69	43.5	36.0	15.3	6.72	2.35	0.810	KURU	KURU
07	1.07	0.856	3.49	6.23	139.	33.1	15.0	6.52	2.35	0.810	KURU	KURU
08	1.18	0.856	3.36	6.23	58.4	164.	13.8	6.33	2.20	0.720	KURU	KURU
09	1.12	0.900	3.24	5.81	38.5	176.	12.9	6.33	2.20	0.660	KURU	KURU
10	1.07	0.900	3.49	7.38	12.6	85.2	11.0	6.13	2.20	0.600	KURU	0.068
11	1.01	0.956	3.61	9.75	539.	61.4	15.0	5.94	2.20	0.530	KURU	0.068
12	1.01	0.956	3.24	13.2	387.	92.2	15.0	5.74	2.20	0.460	KURU	0.068
13	1.01	1.01	2.99	12.6	149.	149.	15.0	5.55	2.20	0.410	KURU	0.086
14	1.01	1.01	2.77	16.8	80.1	138.	15.0	5.55	2.20	0.410	KURU	0.086
15	1.07	0.956	2.77	11.3	52.4	206.	13.5	5.35	2.20	0.300	KURU	0.086
16	1.12	0.956	2.68	8.40	39.0	95.7	13.2	5.15	2.20	0.260	KURU	0.107
17	1.12	0.956	2.68	6.91	35.5	63.7	12.6	4.96	2.20	0.180	KURU	0.107
18	1.07	1.07	2.87	5.94	104.	54.2	12.3	4.76	2.20	0.150	KURU	0.107
19	1.07	1.25	30.3	6.33	203.	119.	12.0	4.56	2.20	0.107	KURU	0.107
20	1.07	2.00	54.3	73.2	153.	69.7	11.8	4.47	2.20	0.068	KURU	0.107
21	1.07	5.81	18.2	48.8	113.	49.4	11.3	4.47	2.20	0.054	KURU	0.107
22	1.12	6.23	11.0	21.9	80.9	41.0	10.8	4.38	2.08	KURU	KURU	0.107
23	1.12	4.86	8.57	21.6	62.0	36.0	10.5	4.29	1.95	KURU	KURU	0.107
24	1.12	4.29	6.92	34.0	52.4	33.1	10.3	4.20	1.83	KURU	KURU	0.107
25	1.12	4.67	6.00	21.2	201.	39.0	9.75	4.02	1.83	KURU	KURU	0.107
26	1.12	52.9	5.24	17.7	339.	30.1	9.50	3.83	1.70	KURU	KURU	0.107
27	1.12	41.7	4.86	15.9	225.	26.4	9.28	3.83	1.60	KURU	KURU	0.150
28	1.18	22.6	4.67	13.8	123.	24.7	8.62	3.65	1.50	KURU	KURU	3.42
29	1.12	15.8	4.29	12.6	-----	23.0	8.40	3.47	1.39	KURU	KURU	3.11
30	1.12	10.5	7.61	11.8	-----	21.6	7.96	3.28	1.27	KURU	KURU	2.65
31	1.12	-----	12.2	11.5	-----	19.4	-----	3.10	-----	KURU	KURU	-----
Maks.	1.68	127.	147.	119.	658.	298.	17.7	7.74	2.95	1.27	KURU	3.42
Min.	0.900	0.812	2.68	5.81	12.3	18.7	7.96	3.10	1.27	KURU	KURU	KURU
Ortalama	1.07	6.31	7.87	16.7	118.	71.6	12.8	5.24	2.15	0.383	KURU	0.366
LT/SN/Km2	0.464	2.73	3.41	7.25	51.3	31.0	5.56	2.27	0.931	0.166	0.000	0.158
AKIM mm.	1.24	7.08	9.13	19.4	124.	83.1	14.4	6.08	2.41	0.444	0.000	0.410
MİL. M3	2.87	16.4	21.1	44.8	287.	192.	33.3	14.0	5.57	1.03	0.000	0.948

SU YILI (2006) YILLIK TOPLAM AKIM 619.02 MİLYON M3 268 MM. 8.5 LT/SN/Km2

03. Susurluk Havzasi

D03A139 Nilüfer Ç. Barakli

YERİ : **Bursada- keles yolu üzerinde bunan doğancı barajına gelinir.keles istikametine devam edilerek 17km sonra nilüfer barajı-**
29°12'7" Doğu - 39°59'40" Kuzey

YAĞIŞ ALANI : 111,30 km2 YAKLAŞIK KOT : 880,54 m

GÖZLEM SÜRESİ : **01.10.2002 - 30.09.2006**

ORTALAMA AKIMLAR : Gözlem süresinde 1.396 m3/sn. (1 Yıllık) 2006 Su yılında 1.396 m3/sn.

ANLIK EN ÇOK VE EN AZ AKIMLAR:

2006 Su yılında anlık ençok akım	:	**16.1**	**m3/sn**	**12.03.2006**
2006 Su yılında anlık enaz akım	:	**0.013**	**m3/sn**	**04.08.2006**
Gözlem süresinde anlık ençok akım	:	**16.1**	**m3/sn**	**12.03.2006**
Gözlem süresinde anlık enaz akım	:	**0.013**	**m3/sn**	**04.08.2006**

İstasyon için kullanılmış anahtar bulunamadı.

Akımlar 01 Ekim 2005 'den 30 Eylül 2006' a kadar m3/sn olarak

Gün	Ekim	Kasım	Aralık	Ocak	Şubat	Mart	Nisan	Mayıs	Haziran	Temmuz	Ağustos	Eylül
01	0.220	0.287	0.770	1.97	0.860	6.95	3.55	2.30	0.420	0.220	0.084	0.030
02	0.420	0.287	0.770	1.97	0.860	6.70	3.38	2.10	0.507	0.220	0.084	0.030
03	0.593	0.287	0.770	1.97	0.860	8.75	3.55	2.10	0.420	0.220	0.054	0.030
04	0.420	0.287	0.680	1.97	0.860	9.45	3.55	2.10	0.420	0.287	0.030	0.030
05	0.353	0.287	0.680	1.97	0.860	7.20	3.55	2.10	0.353	0.220	0.013	0.030
06	0.287	0.287	0.680	1.83	1.09	6.20	3.55	1.97	0.353	0.220	0.013	0.054
07	0.287	0.287	0.680	1.70	1.20	5.95	3.55	1.83	0.353	0.160	0.013	0.054
08	0.287	0.287	0.770	1.70	1.20	5.95	3.55	1.83	0.353	0.160	0.013	0.054
09	0.287	0.287	0.860	1.70	1.20	4.98	3.73	1.83	0.507	0.160	0.013	0.054
10	0.287	0.287	0.860	1.70	1.20	4.33	3.73	1.70	0.593	0.160	0.013	0.054
11	0.287	0.287	0.973	1.70	1.20	4.77	3.73	1.70	0.680	0.122	0.013	0.054
12	0.287	0.287	1.09	1.70	1.20	11.2	3.73	1.58	0.680	0.122	0.013	0.054
13	0.287	0.287	1.33	1.58	1.20	8.10	4.98	1.58	0.680	0.122	0.013	0.054
14	0.287	0.287	1.45	1.58	1.20	7.80	4.33	1.70	0.680	0.122	0.013	0.054
15	0.287	0.287	1.58	1.45	1.20	6.20	3.90	1.58	0.680	0.122	0.013	0.054
16	0.287	0.287	1.70	1.45	1.20	5.20	3.90	1.58	0.680	0.122	0.013	0.054
17	0.287	0.287	1.83	1.33	1.20	4.55	3.73	1.58	0.593	0.122	0.013	0.054
18	0.287	0.287	1.97	1.33	1.20	3.90	3.73	1.45	0.593	0.122	0.013	0.054
19	0.287	0.287	2.10	1.33	1.20	3.73	3.55	1.33	0.507	0.122	0.013	0.054
20	0.287	0.353	2.10	1.20	1.20	3.38	3.55	1.33	0.353	0.122	0.013	0.054
21	0.287	0.353	2.30	1.20	2.10	3.20	3.38	1.09	0.287	0.122	0.013	0.084
22	0.287	0.420	2.30	1.09	3.55	3.20	3.20	1.09	0.220	0.122	0.013	0.084
23	0.287	0.420	2.10	1.09	3.73	3.73	3.03	0.973	0.220	0.122	0.013	0.122
24	0.287	0.507	2.10	1.09	3.90	4.33	3.03	0.680	0.220	0.122	0.013	0.160
25	0.287	0.507	2.10	0.973	7.50	4.12	2.85	0.680	0.220	0.122	0.013	0.122
26	0.287	0.593	1.97	0.973	8.10	3.90	2.68	0.680	0.160	0.084	0.013	0.122
27	0.287	0.593	1.97	0.973	7.20	3.90	2.50	0.680	0.160	0.084	0.013	0.160
28	0.287	0.680	1.97	0.860	6.70	3.90	2.30	0.680	0.220	0.084	0.013	0.220
29	0.287	0.680	1.97	0.860	-----	3.90	2.30	0.593	0.353	0.084	0.013	0.287
30	0.287	0.770	1.97	0.860	-----	3.90	2.30	0.593	0.287	0.084	0.013	0.287
31	0.287	-----	1.97	0.860	-----	3.73	-----	0.507	-----	0.084	0.013	-----
Maks.	0.680	0.770	2.50	2.10	11.9	16.1	5.45	2.30	0.770	0.287	0.084	0.353
Min.	0.220	0.287	0.680	0.860	0.860	3.03	2.30	0.420	0.160	0.084	0.013	0.030
Ortalama	0.305	0.378	1.50	1.42	2.32	5.39	3.41	1.40	0.425	0.141	0.019	0.087
LT/SN/Km2	2.74	3.39	13.4	12.7	20.8	48.4	30.7	12.6	3.82	1.26	0.175	0.781
AKIM mm.	7.35	8.79	36.0	34.1	50.4	130.	79.5	33.8	9.90	3.39	0.468	2.02
MİL. M3	0.818	0.979	4.01	3.80	5.61	14.4	8.85	3.76	1.10	0.377	0.052	0.225

SU YILI (2006) YILLIK TOPLAM AKIM 43.98 MİLYON M3 395 MM. 12.5 LT/SN/Km2

03. Susurluk Havzasi

D03A140 UMURLAR ÇAYI YUSUFÇAMI

YERİ : SINDIRGI İLÇESİ, YUSUFÇAMI ILE UMURLAR KÖYLERI ARASINDAKI KARAYOLU KÖPRÜSÜNÜN 10 M MANSAP TARAFINDADIR.
28°14'48" Doğu - 39°18'25" Kuzey

YAĞIŞ ALANI : 12.71 km2 YAKLAŞIK KOT : 441.38 m

GÖZLEM SÜRESİ : 22.09.2003 - 30.09.2006

ORTALAMA AKIMLAR : Gözlem süresinde 0.068 m3/sn. (3 Yıllık) 2006 Su yılında 0.068 m3/sn.

ANLIK EN ÇOK VE EN AZ AKIMLAR:

2006 Su yılında anlık encok akım	:	6.56	m3/sn	06.02.2006
2006 Su yılında anlık enaz akım	:	0.000	m3/sn	01.10.2005
Gözlem süresinde anlık encok akım	:	28.9	m3/sn	04.07.2005
Gözlem süresinde anlık enaz akım	:	0.000	m3/sn	06.10.2003

Akımlar 01 Ekim 2005 'den 30 Eylül 2006' a kadar m3/sn olarak

Gün	Ekim	Kasım	Aralık	Ocak	Şubat	Mart	Nisan	Mayıs	Haziran	Temmuz	Ağustos	Eylül
01	KURU	0.002	0.028	0.082	0.210	0.082	0.082	0.064	0.002	KURU	KURU	KURU
02	0.002	0.003	0.028	0.064	0.082	0.082	0.082	0.046	0.002	KURU	KURU	KURU
03	0.002	0.003	0.019	0.046	0.082	0.082	0.064	0.046	KURU	KURU	KURU	KURU
04	0.002	0.003	0.019	0.046	0.108	0.082	0.064	0.046	KURU	KURU	KURU	KURU
05	0.002	0.003	0.019	0.046	0.210	0.082	0.064	0.046	KURU	KURU	KURU	KURU
06	0.001	0.003	0.012	0.046	1.67	0.064	0.064	0.046	KURU	KURU	KURU	KURU
07	0.001	0.003	0.012	0.064	0.370	0.082	0.064	0.064	KURU	KURU	KURU	KURU
08	0.001	0.003	0.019	0.064	0.250	0.210	0.064	0.046	KURU	KURU	KURU	KURU
09	0.001	0.002	0.028	0.046	0.250	0.176	0.064	0.046	0.002	KURU	KURU	KURU
10	0.001	0.002	0.019	0.046	0.933	0.142	0.046	0.036	0.004	KURU	KURU	KURU
11	0.001	0.002	0.019	0.046	1.53	0.933	0.046	0.025	0.002	KURU	KURU	KURU
12	0.001	0.005	0.019	0.046	1.07	1.07	0.046	0.046	0.002	KURU	KURU	KURU
13	0.001	0.005	0.012	0.046	0.460	0.310	0.046	0.046	0.004	KURU	KURU	KURU
14	0.001	0.005	0.012	0.036	0.310	0.460	0.064	0.036	0.004	KURU	KURU	KURU
15	0.001	0.005	0.019	0.036	0.250	0.310	0.064	0.036	0.002	KURU	KURU	KURU
16	0.001	0.005	0.054	0.036	0.176	0.310	0.064	0.025	0.004	KURU	KURU	KURU
17	0.001	0.005	0.073	0.036	0.176	0.250	0.046	0.025	0.002	KURU	KURU	KURU
18	0.002	0.028	0.054	0.036	0.176	0.310	0.046	0.018	0.002	KURU	KURU	KURU
19	0.002	0.008	0.176	0.082	0.176	0.370	0.046	0.018	0.002	KURU	KURU	KURU
20	0.002	0.097	0.108	0.142	0.142	0.250	0.046	0.012	KURU	KURU	KURU	KURU
21	0.002	0.073	0.082	0.082	0.142	0.210	0.046	0.009	KURU	KURU	KURU	KURU
22	0.002	0.039	0.082	0.082	0.142	0.142	0.046	0.009	KURU	KURU	KURU	KURU
23	0.002	0.039	0.082	0.176	0.108	0.142	0.036	0.004	KURU	KURU	KURU	KURU
24	0.001	0.028	0.082	0.176	0.082	0.142	0.036	0.002	0.004	KURU	KURU	KURU
25	0.001	0.073	0.082	0.176	0.108	0.142	0.036	0.002	KURU	KURU	KURU	0.002
26	0.002	0.310	0.082	0.142	0.142	0.108	0.025	0.002	KURU	KURU	KURU	0.002
27	0.002	0.157	0.108	0.142	0.142	0.108	0.018	0.002	KURU	KURU	KURU	0.002
28	0.001	0.073	0.082	0.108	0.108	0.108	0.018	0.002	KURU	KURU	KURU	0.002
29	0.001	0.073	0.082	0.108	-----	0.108	0.036	0.002	KURU	KURU	KURU	0.310
30	0.002	0.039	0.082	0.142	-----	0.082	0.046	0.004	KURU	KURU	KURU	0.018
31	0.002	-----	0.082	0.176	-----	0.082	-----	0.002	-----	KURU	KURU	-----
Maks.	0.039	1.80	1.20	0.650	6.56	5.68	0.108	0.560	0.036	KURU	KURU	5.46
Min.	KURU	0.001	0.012	0.025	0.082	0.064	0.018	KURU	KURU	KURU	KURU	KURU
Ortalama	0.001	0.037	0.054	0.084	0.343	0.227	0.051	0.026	0.001	KURU	KURU	0.011
LT/SN/Km2	0.112	2.87	4.26	6.60	27.0	17.8	3.97	2.06	0.100	0.000	0.000	0.881
AKIM mm.	0.299	7.45	11.4	17.7	65.3	47.8	10.3	5.53	0.258	0.000	0.000	2.28
MİL. M3	0.004	0.095	0.145	0.225	0.830	0.607	0.131	0.070	0.003	0.000	0.000	0.029

SU YILI (2006) YILLIK TOPLAM AKIM 2.14 MİLYON M3 168 MM. 5.3 LT/SN/Km2

03. Susurluk Havzasi

D03A141 EĞRİ DERE GÖLCÜK (SINDIRGI)

YERİ : SINDIRGI GÖLCÜK BELDESİ ILE KARAKAYA KÖYÜ ARASINDAKI KARAYOLU KÖPRÜSÜNÜN 75 M MEMBA TARAFINDADIR.
28°0'8" Doğu - 39°17'14" Kuzey

YAĞIŞ ALANI : 39.92 km2 YAKLAŞIK KOT : 275 m

GÖZLEM SÜRESİ : 26.05.2004 - 30.09.2006

ORTALAMA AKIMLAR : Gözlem süresinde 0.441 m3/sn. (1 Yıllık) 2006 Su yılında 0.441 m3/sn.

ANLIK EN ÇOK VE EN AZ AKIMLAR:

2006 Su yılında anlık encok akım	:	27.1	m3/sn	11.03.2006
2006 Su yılında anlık enaz akım	:	0.002	m3/sn	12.08.2006
Gözlem süresinde anlık encok akım	:	27.1	m3/sn	11.03.2006
Gözlem süresinde anlık enaz akım	:	0.002	m3/sn	12.08.2006

Akımlar 01 Ekim 2005 'den 30 Eylül 2006' a kadar m3/sn olarak

Gün	Ekim	Kasım	Aralık	Ocak	Şubat	Mart	Nisan	Mayıs	Haziran	Temmuz	Ağustos	Eylül
01	0.021	0.069	0.275	1.33	0.335	0.995	0.275	0.180	0.035	0.016	0.010	0.010
02	0.035	0.069	0.228	0.738	0.275	0.880	0.275	0.180	0.035	0.016	0.010	0.010
03	0.048	0.069	0.180	0.335	0.520	1.33	0.228	0.180	0.048	0.016	0.003	0.007
04	0.035	0.069	0.135	0.275	0.940	1.05	0.228	0.135	0.048	0.021	0.003	0.010
05	0.048	0.069	0.135	0.228	1.13	0.880	0.180	0.135	0.048	0.021	0.007	0.010
06	0.048	0.069	0.090	0.275	5.35	0.738	0.180	0.135	0.048	0.016	0.010	0.010
07	0.048	0.069	0.090	0.228	2.35	1.27	0.180	0.090	0.048	0.016	0.007	0.007
08	0.048	0.069	0.069	0.180	2.21	2.35	0.135	0.090	0.048	0.016	0.007	0.007
09	0.048	0.069	0.090	0.180	2.21	1.58	0.135	0.090	0.069	0.016	0.010	0.007
10	0.048	0.069	0.090	0.135	6.89	1.43	0.180	0.090	0.090	0.016	0.007	0.007
11	0.048	0.069	0.090	0.135	6.26	2.00	0.180	0.090	0.069	0.016	0.007	0.007
12	0.048	0.069	0.090	0.090	2.51	4.01	0.135	0.180	0.069	0.016	0.003	0.010
13	0.048	0.069	0.069	0.090	2.00	2.83	0.180	0.180	0.069	0.010	0.002	0.010
14	0.048	0.069	0.069	0.069	1.93	3.63	0.180	0.135	0.069	0.010	0.003	0.016
15	0.048	0.069	0.069	0.069	1.93	2.51	0.180	0.090	0.069	0.010	0.007	0.016
16	0.048	0.069	0.090	0.069	1.93	2.07	0.135	0.090	0.069	0.010	0.007	0.016
17	0.048	0.069	0.458	0.048	1.93	1.78	0.135	0.090	0.069	0.007	0.010	0.016
18	0.048	0.395	0.458	0.048	2.14	1.62	0.135	0.090	0.048	0.007	0.007	0.016
19	0.048	0.135	2.28	0.048	2.51	1.53	0.135	0.069	0.048	0.007	0.007	0.021
20	0.048	0.458	1.53	0.228	2.35	1.43	0.090	0.069	0.048	0.007	0.007	0.021
21	0.048	0.228	1.20	0.820	2.21	1.33	0.090	0.069	0.048	0.007	0.007	0.021
22	0.048	0.180	0.820	0.520	2.21	1.27	0.090	0.069	0.035	0.007	0.007	0.021
23	0.048	0.135	0.458	0.458	2.21	1.20	0.090	0.069	0.048	0.010	0.007	0.021
24	0.048	0.275	0.275	0.995	2.21	2.35	0.135	0.048	0.048	0.010	0.010	0.021
25	0.048	0.995	0.228	0.820	2.51	2.59	0.275	0.048	0.048	0.007	0.010	0.035
26	0.069	1.70	0.180	0.655	2.67	2.00	0.275	0.048	0.035	0.010	0.010	0.035
27	0.069	1.58	0.135	0.520	2.00	0.995	0.228	0.048	0.021	0.010	0.007	0.035
28	0.069	1.27	0.135	0.458	2.00	0.520	0.180	0.048	0.016	0.010	0.007	0.048
29	0.069	0.820	0.135	0.458	-----	0.458	0.228	0.048	0.016	0.010	0.003	0.395
30	0.069	0.458	0.090	0.395	-----	0.458	0.228	0.048	0.016	0.010	0.003	0.135
31	0.069	-----	1.53	0.395	-----	0.395	-----	0.048	-----	0.010	0.007	-----
Maks.	0.069	6.58	10.7	2.43	20.5	27.1	0.335	0.458	0.135	0.090	0.021	1.13
Min.	0.021	0.069	0.069	0.048	0.069	0.335	0.069	0.035	0.016	0.003	0.002	0.007
Ortalama	0.050	0.327	0.380	0.364	2.35	1.60	0.177	0.096	0.049	0.012	0.007	0.033
LT/SN/Km2	1.26	8.18	9.51	9.12	58.8	40.0	4.43	2.41	1.23	0.300	0.171	0.836
AKIM mm.	3.38	21.2	25.5	24.4	142.	107.	11.5	6.45	3.19	0.803	0.459	2.17
MİL. M3	0.135	0.847	1.02	0.976	5.68	4.27	0.458	0.257	0.127	0.032	0.018	0.086

SU YILI (2006) YILLIK TOPLAM AKIM 13.91 MİLYON M3 348 MM. 11.0 LT/SN/Km2

04

KUZEY EGE HAVZASI

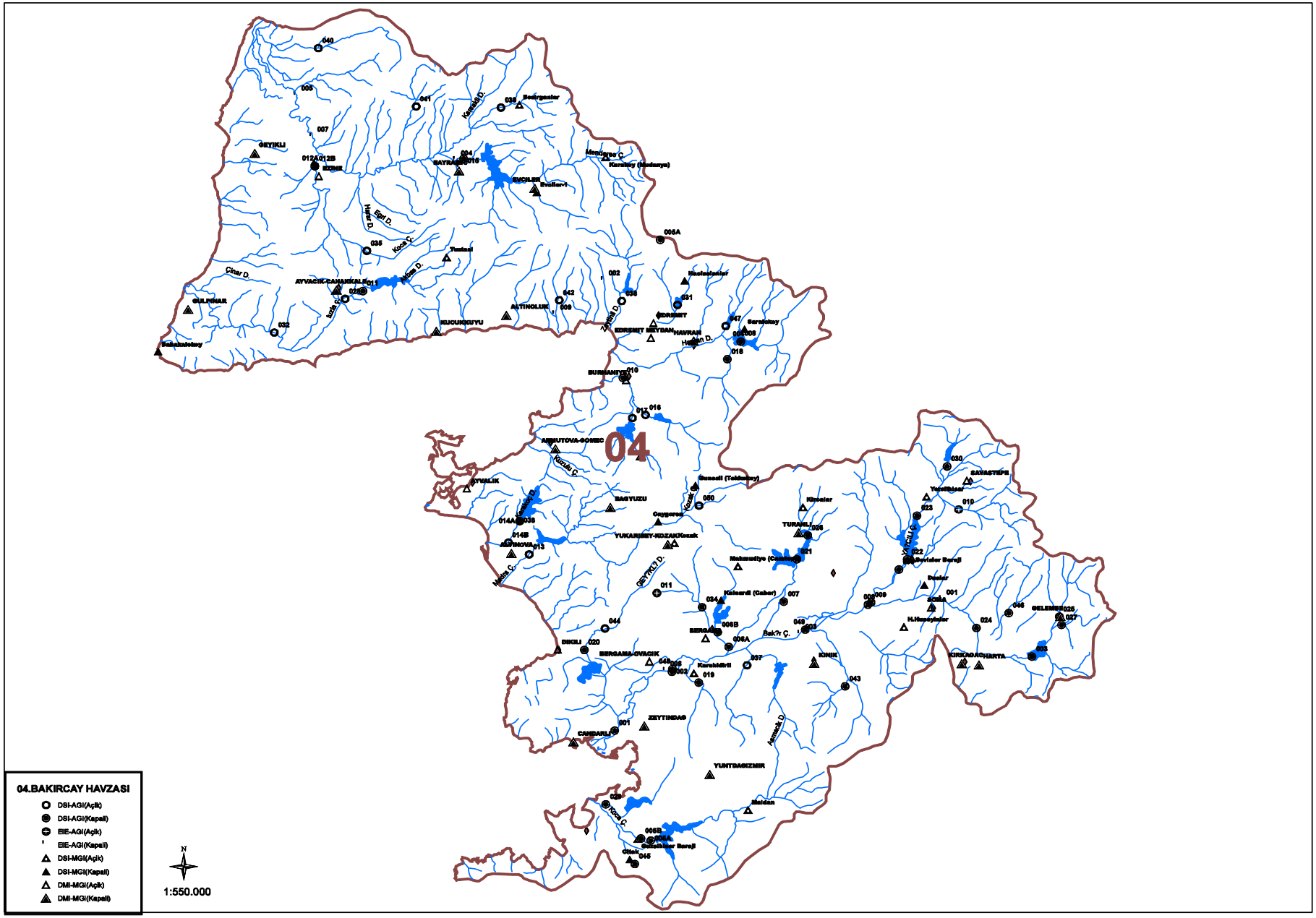
04
04.BAKIRCAY HAVZASI
DSI-AGI(Açlık)
DSI-AGI(Kapalı)
EIE-AGI(Açlık)
EIE-AGI(Kapalı)
DSI-MGI(Açlık)
DSI-MGI(Kapalı)
DMI-MGI(Açlık)
DMI-MGI(Kapalı)
N
1:550.000

04. Kuzey Ege Havzasi

D04A013 MADRA ÇAYI SELİMİYE

YERİ : ALTINOVA DİKİLI KARAYOLUNUN 2. KM SINDEKI KÖPRÜNÜN 300 M MEMBA TARAFINDADIR.
26°48'59" Doğu - 39°12'59" Kuzey

YAĞIŞ ALANI : 426.00 km2 YAKLAŞIK KOT : 24 m

GÖZLEM SÜRESİ : 14.01.1964 - 30.09.2006

ORTALAMA AKIMLAR : Gözlem süresinde 2.705 m3/sn. (35 Yıllık) 2006 Su yılında 0.984 m3/sn.

ANLIK EN ÇOK VE EN AZ AKIMLAR:

2006 Su yılında anlık ençok akım	:	31.4	m3/sn	13.03.2006
2006 Su yılında anlık enaz akım	:	0.138	m3/sn	04.12.2005
Gözlem süresinde anlık ençok akım	:	400.	m3/sn	07.01.1967
Gözlem süresinde anlık enaz akım	:	0.000	m3/sn	13.08.1965

13. Anahtar Eğrisi (Seviyeler cm olarak)

Seviye	Akım	Seviye	Akım	Seviye	Akım	Seviye	Akım
1	0.000	61	6.1	121	37.0	181	89.0
13	0.034	73	10.5	133	45.0	193	100.
25	0.280	85	15.5	145	55.0	207	120.
37	0.960	97	21.0	157	65.0	223	140.
49	2.9	109	29.0	169	77.0	242	165.

Akımlar 01 Ekim 2005 'den 30 Eylül 2006' a kadar m3/sn olarak

Gün	Ekim	Kasım	Aralık	Ocak	Şubat	Mart	Nisan	Mayıs	Haziran	Temmuz	Ağustos	Eylül
01	0.365	0.325	0.185	1.05	1.35	1.35	2.05	0.295	0.410	0.365	0.410	0.630
02	0.470	0.295	0.185	1.05	1.35	1.35	2.05	0.295	0.410	0.410	0.365	0.470
03	0.210	0.295	0.156	1.05	1.35	1.35	2.20	0.295	0.365	0.410	0.410	0.365
04	0.295	0.185	0.156	1.05	1.35	1.35	2.20	0.295	0.410	0.470	0.410	0.410
05	0.210	0.210	0.138	1.05	1.45	1.35	2.20	0.295	0.410	0.325	0.365	0.295
06	0.210	0.185	0.138	1.05	1.68	1.35	2.20	0.470	0.365	0.410	0.365	0.325
07	0.295	0.156	0.138	1.05	1.45	1.45	2.05	0.410	0.410	0.410	0.470	0.295
08	0.255	0.185	0.156	1.05	1.35	1.68	2.35	0.365	0.470	0.410	0.470	0.365
09	0.295	0.156	0.156	1.15	1.25	1.45	2.20	0.410	0.530	0.410	0.710	0.365
10	0.365	0.156	0.156	1.35	1.35	1.35	2.20	0.365	0.530	0.530	0.710	0.410
11	0.365	0.295	0.365	1.35	1.35	1.35	2.20	0.295	0.575	0.470	0.630	0.530
12	0.295	0.295	0.365	1.35	1.25	1.35	2.20	0.295	0.470	0.575	0.630	0.295
13	0.210	0.255	0.410	1.35	1.25	5.84	2.20	0.210	0.410	0.530	0.575	0.325
14	0.365	0.325	0.410	1.35	1.25	19.5	2.20	0.470	0.470	0.470	0.575	0.325
15	0.470	0.470	0.470	1.35	1.25	18.4	2.20	0.575	0.325	0.470	0.575	0.325
16	0.470	0.410	0.470	1.35	1.25	17.3	2.20	0.365	0.410	0.410	0.630	0.325
17	0.325	0.410	0.470	1.35	1.25	15.1	2.20	0.530	0.365	0.575	0.575	0.410
18	0.295	0.365	0.470	1.35	1.25	13.7	2.20	0.470	0.255	0.530	0.530	0.470
19	0.295	0.410	0.470	1.45	1.25	12.1	2.20	0.575	0.325	0.470	0.530	0.530
20	0.325	0.325	0.410	1.35	1.25	5.84	1.45	0.365	0.295	0.470	0.470	0.575
21	0.295	0.210	0.410	1.35	1.25	0.365	0.410	0.325	0.365	0.410	0.470	0.630
22	0.255	0.156	0.410	1.35	1.25	0.255	0.365	0.325	0.295	0.410	0.410	0.710
23	0.295	0.210	0.410	1.35	1.25	0.210	0.365	0.325	0.325	0.410	0.530	0.630
24	0.325	0.210	0.410	1.35	1.35	0.470	0.470	0.410	0.365	0.410	0.530	0.575
25	0.325	0.630	0.410	1.35	1.35	2.05	0.470	0.410	0.295	0.410	0.530	0.410
26	0.255	0.365	0.410	1.35	1.35	2.05	0.470	0.470	0.295	0.410	0.530	0.325
27	0.185	0.410	0.410	1.35	1.35	2.05	0.470	0.410	0.325	0.470	0.530	0.325
28	0.185	0.255	0.410	1.35	1.35	2.05	0.470	0.365	0.255	0.470	0.630	0.530
29	0.365	0.470	0.575	1.35	-----	2.05	0.630	0.295	0.295	0.470	0.575	0.365
30	0.470	0.210	0.470	1.35	-----	2.05	0.325	0.325	0.295	0.410	0.575	0.255
31	0.365	-----	0.800	1.35	-----	2.05	-----	0.325	-----	0.410	0.575	-----
Maks.	1.15	3.40	3.60	2.80	4.20	31.4	7.14	0.800	0.880	0.880	0.960	0.960
Min.	0.156	0.156	0.138	1.05	1.25	0.156	0.295	0.185	0.210	0.255	0.295	0.210
Ortalama	0.313	0.294	0.355	1.27	1.32	4.52	1.58	0.375	0.377	0.445	0.525	0.427
LT/SN/Km2	0.735	0.691	0.833	2.98	3.10	10.6	3.71	0.881	0.886	1.05	1.23	1.00
AKIM mm.	1.97	1.79	2.23	7.98	7.51	28.4	9.61	2.36	2.30	2.80	3.30	2.60
MİL. M3	0.839	0.763	0.950	3.40	3.20	12.1	4.09	1.00	0.978	1.19	1.41	1.11

SU YILI (2006) YILLIK TOPLAM AKIM 31.03 MİLYON M3 73 MM. 2.3 LT/SN/Km2

04. Kuzey Ege Havzasi

D04A016 KARADERE BAHADINLI

YERİ : BAHADİNLI KÖYÜNDEKI KARADERE KÖPRÜSÜNÜN 30 M MANSAP TARAFINDADIR.
27°1'3" Doğu - 39°26'45" Kuzey

YAĞIŞ ALANI : 126.70 km2 YAKLAŞIK KOT : 87 m

GÖZLEM SÜRESİ : 09.07.1964 - 30.09.2006

ORTALAMA AKIMLAR : Gözlem süresinde 0.800 m3/sn. (24 Yıllık) 2006 Su yılında 1.079 m3/sn.

ANLIK EN ÇOK VE EN AZ AKIMLAR:

2006 Su yılında anlık ençok akım	:	25.5	m3/sn	11.02.2006
2006 Su yılında anlık enaz akım	:	0.000	m3/sn	01.09.2006
Gözlem süresinde anlık ençok akım	:	130.	m3/sn	20.02.1965
Gözlem süresinde anlık enaz akım	:	0.000	m3/sn	29.08.1979

10. Anahtar Eğrisi (Seviyeler cm olarak)

Seviye	Akım	Seviye	Akım	Seviye	Akım	Seviye	Akım
10	0.003	16	0.066	40	3.5	60	11.5
11	0.006	20	0.194	44	4.8	70	17.5
12	0.012	25	0.513	48	6.2	90	30.9
13	0.019	30	1.2	50	7.1	100	39.0
14	0.030	35	2.2	54	8.6	115	52.0

Akımlar 01 Ekim 2005 'den 30 Eylül 2006' a kadar m3/sn olarak

Gün	Ekim	Kasım	Aralık	Ocak	Şubat	Mart	Nisan	Mayıs	Haziran	Temmuz	Ağustos	Eylül
01	0.016	0.100	1.10	1.89	1.23	3.50	2.24	1.10	0.300	0.100	0.008	KURU
02	2.06	0.100	1.10	1.71	1.23	2.69	2.24	0.980	0.300	0.100	0.008	KURU
03	0.856	0.100	1.10	1.35	1.23	4.45	2.06	0.980	0.300	0.082	0.005	KURU
04	0.350	0.100	1.10	1.35	1.23	2.96	2.06	0.856	0.427	0.068	0.005	KURU
05	0.140	0.118	1.10	1.23	1.35	2.42	2.06	0.856	0.350	0.068	0.005	KURU
06	0.118	0.118	1.10	1.10	4.13	2.24	1.89	0.733	0.300	0.058	0.005	KURU
07	0.100	0.118	1.10	1.10	2.96	3.82	1.89	0.733	0.250	0.058	0.008	KURU
08	0.100	0.118	1.10	0.980	2.24	8.24	2.42	0.733	0.427	0.047	0.008	KURU
09	0.100	0.118	1.23	0.980	1.89	5.88	2.06	0.733	0.503	0.047	0.008	KURU
10	0.100	0.118	1.23	0.980	10.1	4.45	1.89	0.656	0.503	0.047	0.008	KURU
11	0.100	0.118	1.23	0.856	11.0	4.76	1.71	0.656	0.427	0.047	0.008	KURU
12	0.100	0.140	1.23	0.856	4.45	5.88	1.71	0.656	0.350	0.040	0.008	KURU
13	0.100	0.140	1.53	0.856	2.96	7.10	1.71	0.580	0.503	0.040	0.008	KURU
14	0.100	0.140	1.23	0.856	2.42	7.10	1.53	0.580	0.427	0.040	0.008	KURU
15	0.100	0.140	1.23	0.856	2.24	5.88	1.53	0.580	0.350	0.040	0.008	KURU
16	0.100	0.140	1.23	0.856	1.89	5.13	1.35	0.503	0.350	0.032	0.005	KURU
17	0.100	0.170	1.23	0.733	1.89	4.76	1.35	0.427	0.350	0.032	0.005	KURU
18	0.100	0.656	1.35	0.733	2.06	4.76	1.35	0.427	0.350	0.025	0.005	KURU
19	0.100	0.427	1.71	2.42	2.06	4.45	1.23	0.427	0.300	0.025	0.005	KURU
20	0.100	0.856	1.23	3.50	2.06	4.13	1.23	0.350	0.300	0.025	0.005	KURU
21	0.100	0.503	1.10	2.42	1.89	3.82	1.23	0.350	0.200	0.025	0.005	KURU
22	0.100	0.427	0.980	2.06	1.71	3.50	1.23	0.350	0.170	0.018	0.005	KURU
23	0.100	0.427	0.856	2.06	1.71	2.96	1.10	0.300	0.140	0.018	0.005	KURU
24	0.100	0.656	0.733	1.89	1.89	3.50	1.10	0.350	0.118	0.018	0.005	0.040
25	0.100	4.76	0.733	1.71	5.88	3.23	0.980	0.427	0.118	0.013	0.005	0.082
26	0.100	2.24	0.733	1.53	4.76	2.96	0.980	0.300	0.100	0.013	0.005	0.058
27	0.100	1.89	0.656	1.35	4.76	2.96	0.980	0.350	0.100	0.013	0.005	0.058
28	0.100	1.53	0.856	1.35	3.82	2.96	0.980	0.350	0.100	0.013	0.005	0.058
29	0.100	1.53	1.35	1.35	-----	2.69	1.10	0.350	0.100	0.013	0.005	0.068
30	0.100	1.23	1.35	1.35	-----	2.42	0.980	0.427	0.100	0.013	0.005	0.058
31	0.100	-----	2.24	1.23	-----	2.24	-----	0.350	-----	0.013	0.005	-----
Maks.	19.5	16.9	3.82	12.1	25.5	15.1	7.10	1.10	1.23	0.140	0.047	4.13
Min.	0.016	0.100	0.656	0.733	1.23	2.24	0.856	0.300	0.058	0.008	0.005	KURU
Ortalama	0.195	0.641	1.16	1.40	3.11	4.12	1.54	0.563	0.287	0.038	0.006	0.014
LT/SN/Km2	1.54	5.06	9.18	11.1	24.5	32.5	12.1	4.44	2.27	0.303	0.048	0.111
AKIM mm.	4.12	13.1	24.6	29.7	59.4	87.2	31.5	11.9	5.87	0.812	0.128	0.288
MİL. M3	0.522	1.66	3.11	3.76	7.52	11.0	3.99	1.51	0.744	0.103	0.016	0.036

SU YILI (2006) YILLIK TOPLAM AKIM 33.97 MİLYON M3 268 MM. 8.5 LT/SN/Km2

04. Kuzey Ege Havzasi

D04A017 KARINCA DERE REŞİTKÖY

YERİ : BURHANİYE - REŞITKÖY KARAYOLUNUN 10. KM SINDEKI KÖPRÜNÜN 100 M MEMBAINDADIR.
26°59'34" Doğu - 39°26'23" Kuzey

YAĞIŞ ALANI : 112.40 km2 YAKLAŞIK KOT : 83 m

GÖZLEM SÜRESİ : 10.07.1964 - 30.09.2006

ORTALAMA AKIMLAR : Gözlem süresinde 0.747 m3/sn. (41 Yıllık) 2006 Su yılında 0.879 m3/sn.

ANLIK EN ÇOK VE EN AZ AKIMLAR:

2006 Su yılında anlık ençok akım	:	38.8	m3/sn	11.02.2006
2006 Su yılında anlık enaz akım	:	0.000	m3/sn	01.10.2005
Gözlem süresinde anlık ençok akım	:	300.	m3/sn	05.02.2003
Gözlem süresinde anlık enaz akım	:	0.000	m3/sn	01.07.1965

32. Anahtar Eğrisi (Seviyeler cm olarak)

Seviye	Akım	Seviye	Akım	Seviye	Akım	Seviye	Akım
1	0.000	20	0.930	42	6.4	270	166.
3	0.000	22	1.3	50	9.3	350	242.
8	0.021	24	1.6	100	35.4	361	0.000
13	0.210	28	2.5	180	90.2	410	320.
18	0.690	33	3.7	220	122.	411	0.000

Akımlar 01 Ekim 2005 'den 30 Eylül 2006' a kadar m3/sn olarak

Gün	Ekim	Kasım	Aralık	Ocak	Şubat	Mart	Nisan	Mayıs	Haziran	Temmuz	Ağustos	Eylül
01	KURU	0.044	1.19	1.78	1.43	3.05	1.28	0.580	0.162	0.044	KURU	KURU
02	0.162	0.044	1.09	1.54	1.31	2.66	1.28	0.580	0.162	0.044	KURU	KURU
03	0.067	0.044	1.09	1.43	1.31	4.60	1.28	0.580	0.115	0.021	KURU	KURU
04	0.021	0.044	0.986	1.43	1.31	3.44	1.28	0.580	0.115	0.014	KURU	KURU
05	0.014	0.044	0.986	1.31	1.31	2.86	1.28	0.580	0.067	0.014	KURU	KURU
06	0.014	0.044	0.986	1.31	3.64	2.66	1.10	0.470	0.115	0.006	KURU	KURU
07	0.006	0.044	0.986	1.31	2.66	3.64	1.10	0.470	0.067	0.006	KURU	KURU
08	0.006	0.044	1.09	1.19	2.13	6.75	2.50	0.470	0.115	0.006	KURU	KURU
09	0.006	0.044	1.19	1.19	1.96	3.98	1.80	0.470	0.115	0.006	KURU	KURU
10	0.006	0.044	1.09	1.19	10.2	2.90	1.28	0.470	0.210	0.006	KURU	KURU
11	0.006	0.044	0.986	1.19	11.6	2.70	1.28	0.360	0.162	0.006	KURU	KURU
12	0.014	0.044	0.986	1.19	4.84	2.90	1.10	0.360	0.285	0.006	KURU	KURU
13	0.014	0.044	0.986	1.19	3.44	3.98	1.10	0.360	0.210	0.006	KURU	KURU
14	0.014	0.044	0.986	1.09	2.86	4.80	1.10	0.360	0.162	0.006	KURU	KURU
15	0.014	0.044	1.09	1.09	2.48	3.98	1.10	0.360	0.162	0.006	KURU	KURU
16	0.014	0.044	1.09	1.09	2.31	3.17	0.930	0.285	0.162	0.004	KURU	KURU
17	0.014	0.067	1.09	1.09	2.31	2.70	0.930	0.285	0.162	0.004	KURU	KURU
18	0.021	0.360	1.43	1.09	2.13	3.43	0.930	0.285	0.162	0.004	KURU	KURU
19	0.021	0.210	2.31	1.96	2.13	3.43	0.810	0.285	0.115	0.004	KURU	KURU
20	0.021	0.470	1.54	2.66	1.96	2.50	0.810	0.285	0.115	0.004	KURU	KURU
21	0.044	0.210	1.31	1.78	1.96	2.20	0.810	0.285	0.115	0.002	KURU	KURU
22	0.044	0.162	1.19	1.66	1.96	2.00	0.810	0.210	0.067	0.002	KURU	KURU
23	0.021	0.162	1.19	1.78	1.78	1.80	0.690	0.210	0.067	0.002	KURU	KURU
24	0.021	0.285	1.09	1.66	2.13	2.20	0.690	0.210	0.067	0.002	KURU	KURU
25	0.021	2.86	1.09	1.66	5.93	2.20	0.690	0.162	0.067	0.002	KURU	KURU
26	0.021	1.96	1.09	1.54	4.12	1.80	0.580	0.162	0.067	0.002	KURU	KURU
27	0.021	1.66	1.09	1.54	4.60	1.60	0.580	0.162	0.044	0.002	KURU	KURU
28	0.021	1.43	1.19	1.43	3.44	1.60	0.580	0.162	0.021	0.002	KURU	KURU
29	0.021	1.54	1.43	1.43	-----	1.45	0.690	0.162	0.021	0.002	KURU	KURU
30	0.021	1.31	1.31	1.43	-----	1.45	0.690	0.162	0.021	0.002	KURU	KURU
31	0.044	-----	2.48	1.43	-----	1.28	-----	0.162	-----	0.002	KURU	-----
Maks.	2.90	15.4	7.12	5.38	38.8	14.9	6.75	0.580	0.470	0.044	0.004	0.002
Min.	KURU	0.044	0.986	1.09	1.31	1.28	0.580	0.162	0.021	0.002	KURU	KURU
Ortalama	0.024	0.446	1.21	1.44	3.19	2.89	1.04	0.339	0.117	0.008	KURU	KURU
LT/SN/Km2	0.217	3.97	10.8	12.8	28.4	25.7	9.22	3.02	1.04	0.069	0.000	0.000
AKIM mm.	0.580	10.3	28.9	34.3	68.6	69.0	23.9	8.09	2.69	0.184	0.000	0.000
MİL. M3	0.065	1.16	3.25	3.86	7.71	7.75	2.69	0.909	0.302	0.021	0.000	0.000

SU YILI (2006) YILLIK TOPLAM AKIM 27.72 MİLYON M3 247 MM. 7.8 LT/SN/Km2

04. Kuzey Ege Havzasi

D04A021 İLYA D. ÇALTIKORU

YERİ : BERGAMA TURANLI YOLUNUN 13.KM'SİNDEN SAĞA AYRILAN YOLUN ÜZERİNDEKİ ÇALTIKORU KÖYÜNDEDİR
(PAFTA L18 C1)
27°19'48" Doğu - 39°13'24" Kuzey

YAĞIŞ ALANI : 118,90 km2 YAKLAŞIK KOT : 100 m

GÖZLEM SÜRESİ : 17.02.1969 - 30.09.2006

ORTALAMA AKIMLAR : Gözlem süresinde 1.188 m3/sn. (26 Yıllık) 2006 Su yılında 1.560 m3/sn.

ANLIK EN ÇOK VE EN AZ AKIMLAR:

2006 Su yılında anlık ençok akım	:	40.3	m3/sn	11.03.2006
2006 Su yılında anlık enaz akım	:	0.000	m3/sn	05.09.2006
Gözlem süresinde anlık ençok akım	:	175.	m3/sn	03.12.1976
Gözlem süresinde anlık enaz akım	:	0.000	m3/sn	29.07.1972

19. Anahtar Eğrisi (Seviyeler cm olarak)

Seviye	Akım	Seviye	Akım	Seviye	Akım	Seviye	Akım
27	0.000	56	0.029	90	1.6	221	33.4
39	0.000	59	0.051	120	7.4	241	39.3
47	0.001	62	0.085	139	12.2	270	48.5
50	0.005	65	0.134	170	19.4	291	54.4
53	0.014	69	0.233	200	27.7		

Akımlar 01 Ekim 2005 'den 30 Eylül 2006' a kadar m3/sn olarak

Gün	Ekim	Kasım	Aralık	Ocak	Şubat	Mart	Nisan	Mayıs	Haziran	Temmuz	Ağustos	Eylül
01	2.73	0.088	2.19	2.54	2.28	3.67	4.05	0.867	0.137	0.003	0.003	0.026
02	3.38	0.103	2.19	2.02	2.36	3.75	4.05	0.782	0.137	0.002	0.006	0.528
03	3.01	0.103	2.19	1.76	2.36	3.84	4.05	0.698	0.103	0.002	0.014	0.426
04	3.60	0.103	2.19	1.59	4.50	4.24	4.05	0.698	0.103	0.002	0.014	0.374
05	4.16	0.103	2.19	1.53	5.20	3.92	4.05	0.613	0.103	0.002	0.016	0.012
06	4.28	0.103	2.19	1.59	4.83	3.75	2.36	0.613	0.088	0.001	0.014	0.002
07	4.28	0.103	2.19	1.40	4.83	6.13	1.33	0.613	0.088	0.001	0.014	0.019
08	4.28	0.088	2.19	1.40	4.24	8.46	1.40	0.613	0.057	0.002	0.014	0.103
09	4.28	0.088	2.19	1.33	3.92	4.50	1.33	0.613	0.041	0.002	0.014	0.272
10	4.28	0.103	2.19	1.27	3.92	3.72	1.27	0.613	0.041	0.001	0.014	0.238
11	4.39	0.088	2.19	1.27	3.84	10.2	1.27	0.528	0.026	0.001	0.012	0.426
12	4.50	0.103	2.19	1.27	3.92	8.34	1.21	0.528	0.026	0.002	0.009	1.02
13	4.61	0.103	2.19	1.21	3.84	7.31	1.21	0.528	0.041	0.002	0.003	1.02
14	4.50	0.103	1.33	1.21	3.75	6.29	1.21	0.477	0.041	0.002	0.041	0.613
15	4.28	0.103	0.477	1.14	3.75	4.61	1.14	0.477	0.019	0.002	0.088	0.613
16	4.05	0.103	0.426	1.08	3.67	4.05	1.08	0.426	0.019	0.001	0.072	0.613
17	3.94	0.103	0.426	1.08	3.67	3.83	1.08	0.426	0.019	0.001	0.057	0.698
18	3.94	0.374	1.14	1.08	3.58	4.39	1.02	0.426	0.016	0.001	0.057	0.867
19	3.94	0.782	2.28	2.82	3.67	4.16	1.02	0.528	0.014	0.001	0.057	1.27
20	3.94	1.02	1.33	2.54	3.75	4.16	1.02	0.426	0.012	0.001	0.041	1.02
21	3.94	0.323	1.14	1.93	3.58	4.16	1.02	0.374	0.009	0.002	0.041	0.952
22	3.94	0.323	1.08	1.76	3.58	4.16	0.952	0.323	0.009	0.006	0.041	0.952
23	1.33	0.272	1.02	3.19	3.50	4.16	0.952	0.323	0.009	0.006	0.041	1.02
24	0.072	0.528	1.02	2.19	3.50	4.16	0.867	0.238	0.009	0.006	0.041	1.93
25	0.072	1.08	0.867	2.11	3.50	4.16	0.782	0.238	0.006	0.003	0.041	2.36
26	0.072	2.82	0.867	1.93	3.50	4.05	0.782	0.204	0.003	0.003	0.026	2.19
27	0.072	3.60	0.867	1.76	3.42	4.05	0.698	0.171	0.006	0.003	0.016	2.45
28	0.072	2.28	1.08	1.76	3.42	4.05	0.698	0.137	0.006	0.003	0.016	4.05
29	0.072	2.28	4.05	2.02	-----	4.05	0.867	0.137	0.003	0.003	0.026	3.83
30	0.088	2.19	2.64	2.02	-----	4.05	0.867	0.137	0.003	0.003	0.003	3.72
31	0.088	-----	5.28	2.28	-----	4.05	-----	0.137	-----	0.003	0.001	-----
Maks.	4.72	21.8	11.0	4.05	5.20	40.3	4.28	0.952	0.238	0.006	0.477	6.63
Min.	0.057	0.088	0.323	1.08	2.28	3.67	0.698	0.137	0.002	0.001	0.001	KURU
Ortalama	2.91	0.652	1.80	1.74	3.71	4.79	1.59	0.449	0.040	0.002	0.028	1.12
LT/SN/Km2	24.5	5.48	15.1	14.7	31.2	40.3	13.4	3.77	0.335	0.020	0.231	9.42
AKIM mm.	65.5	14.2	40.5	39.3	75.5	108.	34.7	10.1	0.868	0.053	0.620	24.4
MİL. M3	7.79	1.69	4.82	4.67	8.98	12.8	4.12	1.20	0.103	0.006	0.074	2.90

SU YILI (2006) YILLIK TOPLAM AKIM 49.15 MİLYON M3 413 MM. 13.1 LT/SN/Km2

04. Kuzey Ege Havzasi

D04A026 YORTANLI D. PAŞAILICASI

YERİ : BERGAMA TURANLI YOLUNUN 22. KM SİNDEKİ PAŞAILICASI KÖPRÜSÜNDEDİR.(PAFTA J18 C1)
27°19'50" Doğu - 39°13'7" Kuzey

YAĞIŞ ALANI : 101,58 km2 YAKLAŞIK KOT : 85 m

GÖZLEM SÜRESİ : 10.07.1970 - 30.09.2006

ORTALAMA AKIMLAR : Gözlem süresinde 1.079 m3/sn. (22 Yıllık) 2006 Su yılında 0.765 m3/sn.

ANLIK EN ÇOK VE EN AZ AKIMLAR:

2006 Su yılında anlık ençok akım	:	26.1	m3/sn	25.11.2005
2006 Su yılında anlık enaz akım	:	0.000	m3/sn	01.10.2005
Gözlem süresinde anlık ençok akım	:	170.	m3/sn	22.10.1972
Gözlem süresinde anlık enaz akım	:	0.000	m3/sn	01.09.1973

İstasyon için kullanılmış anahtar bulunamadı.

Akımlar 01 Ekim 2005 'den 30 Eylül 2006' a kadar m3/sn olarak

Gün	Ekim	Kasım	Aralık	Ocak	Şubat	Mart	Nisan	Mayıs	Haziran	Temmuz	Ağustos	Eylül
01	KURU	KURU	0.269	1.76	0.428	0.930	2.10	0.612	0.284	0.018	0.018	KURU
02	KURU	KURU	0.130	1.17	0.428	2.10	2.10	0.565	0.237	0.045	0.018	KURU
03	KURU	KURU	0.117	0.876	0.348	4.57	1.97	0.519	0.237	0.128	0.010	KURU
04	KURU	KURU	0.117	0.731	0.348	3.65	1.84	0.519	0.237	0.128	0.010	KURU
05	KURU	KURU	0.117	0.586	0.348	3.31	1.71	0.519	0.237	0.100	0.006	KURU
06	KURU	KURU	0.104	0.586	3.99	3.09	1.45	0.519	0.210	0.045	0.002	KURU
07	KURU	KURU	0.104	0.507	2.21	5.75	1.32	0.519	0.210	0.073	0.001	KURU
08	KURU	KURU	0.117	0.428	2.10	8.66	1.45	0.519	0.237	0.045	KURU	KURU
09	KURU	KURU	0.117	0.348	1.97	5.39	1.32	0.519	0.237	0.014	0.001	KURU
10	KURU	KURU	0.104	0.348	1.84	4.80	1.06	0.472	0.237	0.018	KURU	KURU
11	KURU	KURU	0.104	0.348	1.45	10.9	1.06	0.472	0.237	0.014	KURU	KURU
12	KURU	KURU	0.104	0.348	0.930	10.5	0.930	0.472	0.237	0.014	KURU	KURU
13	KURU	KURU	0.104	0.269	0.930	9.52	0.930	0.472	0.237	0.014	KURU	KURU
14	KURU	KURU	0.104	0.269	0.800	9.69	0.930	0.425	0.237	0.014	KURU	KURU
15	KURU	KURU	0.104	0.269	0.706	6.95	0.800	0.425	0.210	0.014	KURU	KURU
16	KURU	KURU	0.104	0.269	0.753	5.98	0.753	0.425	0.210	0.014	KURU	KURU
17	KURU	KURU	0.117	0.269	0.753	5.27	0.753	0.378	0.210	0.014	KURU	KURU
18	KURU	KURU	0.731	0.269	0.753	5.63	0.753	0.425	0.182	0.010	KURU	KURU
19	KURU	KURU	1.76	2.08	0.659	4.92	0.706	0.425	0.182	0.010	KURU	KURU
20	KURU	KURU	0.586	1.31	0.659	4.22	0.706	0.425	0.182	0.010	KURU	KURU
21	KURU	KURU	0.428	0.586	0.612	3.88	0.706	0.378	0.182	0.010	KURU	KURU
22	KURU	KURU	0.348	0.507	0.659	3.65	0.659	0.378	0.155	0.010	KURU	KURU
23	KURU	KURU	0.269	1.92	0.659	3.43	0.659	0.378	0.155	0.014	KURU	KURU
24	KURU	KURU	0.269	0.731	0.706	4.92	0.612	0.331	0.128	0.014	KURU	KURU
25	KURU	5.63	0.130	0.731	0.753	3.88	0.612	0.331	0.100	0.014	KURU	0.002
26	KURU	2.40	0.130	0.586	0.706	3.31	0.612	0.331	0.100	0.014	KURU	0.006
27	KURU	3.77	0.130	0.507	0.706	3.09	0.612	0.331	0.073	0.014	KURU	0.014
28	KURU	1.02	0.348	0.428	0.659	2.87	0.565	0.331	0.045	0.018	KURU	0.565
29	KURU	0.507	3.77	0.428	-----	2.65	0.565	0.284	0.045	0.018	KURU	0.659
30	KURU	0.348	1.46	0.428	-----	2.54	0.612	0.284	0.018	0.018	KURU	0.706
31	KURU	-----	0.348	0.428	-----	2.21	-----	0.284	-----	0.018	KURU	-----
Maks.	KURU	26.1	10.7	5.04	9.18	19.6	2.21	0.659	0.425	0.155	0.018	0.706
Min.	KURU	KURU	0.091	0.269	0.348	0.930	0.565	0.284	0.018	0.010	KURU	KURU
Ortalama	KURU	0.456	0.411	0.655	0.995	4.91	1.03	0.428	0.183	0.029	0.002	0.065
LT/SN/Km2	0.000	4.49	4.05	6.45	9.80	48.4	10.1	4.21	1.80	0.287	0.021	0.641
AKIM mm.	0.000	11.6	10.8	17.3	23.7	130.	26.2	11.3	4.67	0.769	0.056	1.66
MİL. M3	0.000	1.18	1.10	1.76	2.41	13.2	2.67	1.15	0.474	0.078	0.006	0.169

SU YILI (2006) YILLIK TOPLAM AKIM 24.20 MİLYON M3 238 MM. 7.5 LT/SN/Km2

04. Kuzey Ege Havzasi

D04A028 TUZLA ÇAYI AYVACİK

YERİ : **AYVACIK - SAZLIK KARAYOLUN 2,5. KM SİNDEDIR.**
26°25'1" Doğu - 39°35'11" Kuzey

YAĞIŞ ALANI : 173.30 km2 YAKLAŞIK KOT : 234 m

GÖZLEM SÜRESİ : **25.03.1972 - 30.09.2006**

ORTALAMA AKIMLAR : Gözlem süresinde 1.563 m3/sn. (27 Yıllık) 2006 Su yılında 2.912 m3/sn.

ANLIK EN ÇOK VE EN AZ AKIMLAR:

2006 Su yılında anlık ençok akım	:	**273.**	**m3/sn**	**25.11.2005**
2006 Su yılında anlık enaz akım	:	**0.000**	**m3/sn**	**29.07.2006**
Gözlem süresinde anlık ençok akım	:	**440.**	**m3/sn**	**15.02.1974**
Gözlem süresinde anlık enaz akım	:	**0.000**	**m3/sn**	**01.10.1983**

Akımlar 01 Ekim 2005 'den 30 Eylül 2006' a kadar m3/sn olarak

Gün	Ekim	Kasım	Aralık	Ocak	Şubat	Mart	Nisan	Mayıs	Haziran	Temmuz	Ağustos	Eylül
01	0.016	0.097	1.80	15.0	1.80	4.00	1.37	0.498	0.252	0.097	KURU	KURU
02	1.01	0.097	1.15	9.75	1.58	3.23	1.37	0.498	0.252	0.097	KURU	KURU
03	0.134	0.097	1.01	7.63	1.37	3.23	1.37	0.498	0.170	0.061	KURU	KURU
04	0.061	0.097	0.865	7.10	1.37	2.66	1.37	0.498	0.170	0.097	KURU	KURU
05	0.061	0.097	0.723	5.55	1.58	2.37	1.37	0.416	0.170	0.097	KURU	KURU
06	0.043	0.061	0.723	5.94	16.2	2.09	1.15	0.416	0.170	0.097	KURU	KURU
07	0.043	0.061	0.580	4.00	5.55	74.5	1.15	0.416	0.170	0.097	KURU	KURU
08	0.022	0.097	1.01	3.23	4.00	30.5	1.37	0.416	0.252	0.061	KURU	KURU
09	0.022	0.097	1.01	2.66	3.23	13.7	1.15	0.416	0.252	0.061	KURU	KURU
10	0.022	0.097	0.723	2.37	4.39	9.75	1.15	0.416	0.252	0.061	KURU	KURU
11	0.022	0.097	0.723	2.09	4.00	15.0	1.01	0.498	0.252	0.043	KURU	KURU
12	0.043	0.097	0.580	1.80	3.23	31.9	1.15	0.498	0.252	0.043	KURU	KURU
13	0.022	0.061	0.580	1.80	2.37	31.2	1.01	0.498	0.252	0.061	KURU	KURU
14	0.022	0.097	0.580	1.58	2.37	23.8	1.01	0.498	0.252	0.061	KURU	KURU
15	0.022	0.097	0.580	1.37	1.80	13.7	1.01	0.498	0.170	0.061	KURU	KURU
16	0.022	0.097	0.723	1.37	1.58	11.3	0.865	0.498	0.170	0.043	KURU	KURU
17	0.022	0.134	1.01	1.15	1.58	8.16	0.865	0.416	0.170	0.022	KURU	KURU
18	0.022	0.334	11.3	1.15	1.58	9.22	0.865	0.498	0.170	0.022	KURU	KURU
19	0.022	0.334	7.63	4.00	1.58	6.71	0.723	0.416	0.134	0.022	KURU	KURU
20	0.022	0.416	2.37	4.39	2.09	5.55	0.723	0.416	0.134	0.022	KURU	KURU
21	0.022	0.252	1.58	2.66	1.80	4.78	0.723	0.416	0.134	0.022	KURU	KURU
22	0.022	0.170	1.15	2.37	1.58	4.00	0.580	0.334	0.134	0.016	KURU	KURU
23	0.022	0.865	1.01	2.66	1.37	3.62	0.580	0.334	0.134	0.016	KURU	KURU
24	0.022	76.2	0.865	1.80	1.58	3.23	0.580	0.334	0.134	0.009	KURU	KURU
25	0.022	105.	0.723	1.80	17.5	2.94	0.498	0.334	0.097	0.005	KURU	0.009
26	0.022	11.3	0.723	1.80	8.16	2.37	0.498	0.334	0.097	KURU	KURU	0.016
27	0.043	16.9	5.55	1.58	7.10	2.37	0.498	0.252	0.097	KURU	KURU	0.009
28	0.061	7.10	15.0	1.37	5.17	2.09	0.498	0.252	0.134	KURU	KURU	0.009
29	0.061	4.78	72.8	1.37	-----	1.80	0.498	0.252	0.097	KURU	KURU	2.98
30	0.061	2.66	38.2	1.37	-----	1.80	0.498	0.252	0.097	KURU	KURU	0.577
31	0.061	-----	64.5	1.58	-----	1.58	-----	0.252	-----	KURU	KURU	-----
Maks.	16.9	273.	178.	20.9	37.5	222.	1.58	0.580	0.334	0.134	KURU	29.8
Min.	0.009	0.043	0.580	1.01	1.01	1.37	0.498	0.170	0.097	KURU	KURU	KURU
Ortalama	0.068	7.60	7.67	3.36	3.84	10.7	0.917	0.405	0.174	0.042	KURU	0.120
LT/SN/Km2	0.390	43.8	44.3	19.4	22.2	62.0	5.29	2.34	1.00	0.241	0.000	0.692
AKIM mm.	1.04	114.	119.	52.0	53.6	166.	13.7	6.27	2.60	0.645	0.000	1.79
MİL. M3	0.181	19.7	20.5	9.01	9.29	28.8	2.38	1.09	0.451	0.112	0.000	0.311

SU YILI (2006) YILLIK TOPLAM AKIM 91.82 MİLYON M3 530 MM. 16.8 LT/SN/Km2

04. Kuzey Ege Havzasi

D04A031 EYBEK DERESİ ÇAMCI

YERİ : EDREMİT-ÇAMCI KÖYÜNÜN 1 KM DOĞUSUNDADIR.
27°3'43" Doğu - 39°37'8" Kuzey

YAĞIŞ ALANI : 25.93 km2 YAKLAŞIK KOT : 80 m

GÖZLEM SÜRESİ : 14.01.1977 - 30.09.2006

ORTALAMA AKIMLAR : Gözlem süresinde 0.278 m3/sn. (27 Yıllık) 2006 Su yılında 0.361 m3/sn.

ANLIK EN ÇOK VE EN AZ AKIMLAR:

2006 Su yılında anlık ençok akım	:	12.0	m3/sn	10.02.2006
2006 Su yılında anlık enaz akım	:	0.000	m3/sn	01.10.2005
Gözlem süresinde anlık ençok akım	:	62.0	m3/sn	17.11.1981
Gözlem süresinde anlık enaz akım	:	0.000	m3/sn	09.05.1981

3. Anahtar Eğrisi (Seviyeler cm olarak)

Seviye	Akım	Seviye	Akım	Seviye	Akım	Seviye	Akım
1	0.000	42	4.7	82	18.0	122	37.0
9	0.000	50	6.8	90	21.0	130	41.0
18	0.250	58	9.2	98	25.0	138	46.0
26	1.3	66	12.0	106	29.0	146	51.0
34	2.9	74	14.5	114	33.0	155	58.0

Akımlar 01 Ekim 2005 'den 30 Eylül 2006' a kadar m3/sn olarak

Gün	Ekim	Kasım	Aralık	Ocak	Şubat	Mart	Nisan	Mayıs	Haziran	Temmuz	Ağustos	Eylül
01	KURU	KURU	KURU	0.850	0.450	1.30	0.850	0.340	0.105	0.053	KURU	KURU
02	KURU	KURU	KURU	0.580	0.450	1.30	0.850	0.340	0.105	0.053	KURU	KURU
03	KURU	KURU	0.001	0.450	0.580	2.00	0.850	0.340	0.105	0.053	KURU	KURU
04	KURU	KURU	0.002	0.450	0.580	1.50	0.850	0.340	0.105	0.053	KURU	KURU
05	KURU	KURU	0.022	0.450	0.580	1.30	0.850	0.250	0.105	0.053	KURU	KURU
06	KURU	KURU	0.105	0.450	1.70	1.15	0.850	0.250	0.105	0.053	KURU	KURU
07	KURU	KURU	0.105	0.340	1.00	3.10	0.850	0.250	0.105	0.053	KURU	KURU
08	KURU	KURU	0.105	0.250	0.850	3.20	0.850	0.250	0.105	0.053	KURU	KURU
09	KURU	KURU	0.105	0.250	0.850	1.85	0.580	0.250	0.105	0.053	KURU	KURU
10	KURU	KURU	0.053	0.250	3.10	1.70	0.580	0.250	0.105	0.053	KURU	KURU
11	KURU	KURU	0.053	0.250	3.10	1.70	0.580	0.250	0.105	0.053	KURU	KURU
12	KURU	KURU	0.053	0.250	1.70	1.70	0.580	0.250	0.105	0.053	KURU	KURU
13	KURU	KURU	0.053	0.250	1.30	1.70	0.580	0.250	0.105	0.053	KURU	KURU
14	KURU	KURU	0.053	0.250	1.00	1.85	0.580	0.250	0.105	0.053	KURU	KURU
15	KURU	KURU	0.053	0.250	1.00	1.70	0.450	0.175	0.105	0.022	KURU	KURU
16	KURU	KURU	0.053	0.250	1.00	1.50	0.450	0.175	0.105	0.022	KURU	KURU
17	KURU	KURU	0.105	0.250	1.00	1.30	0.450	0.175	0.105	0.022	KURU	KURU
18	KURU	KURU	0.105	0.250	1.00	1.50	0.450	0.175	0.105	0.022	KURU	KURU
19	KURU	KURU	0.250	1.85	1.00	1.30	0.450	0.175	0.105	KURU	KURU	KURU
20	KURU	0.001	0.175	1.15	1.50	1.30	0.340	0.175	0.105	KURU	KURU	KURU
21	KURU	KURU	0.105	0.850	1.15	1.15	0.340	0.175	0.105	KURU	KURU	KURU
22	KURU	KURU	0.105	0.720	1.00	1.00	0.340	0.175	0.105	KURU	KURU	KURU
23	KURU	KURU	0.105	0.580	1.00	1.00	0.340	0.175	0.105	KURU	KURU	KURU
24	KURU	0.250	0.105	0.580	1.15	1.00	0.340	0.175	0.105	KURU	KURU	KURU
25	KURU	1.15	0.105	0.450	2.60	1.00	0.340	0.105	0.105	KURU	KURU	KURU
26	KURU	0.580	0.105	0.450	2.40	1.00	0.340	0.105	0.105	KURU	KURU	KURU
27	KURU	0.250	0.105	0.450	1.85	1.00	0.340	0.105	0.105	KURU	KURU	KURU
28	KURU	0.022	0.175	0.450	1.50	1.00	0.340	0.105	0.105	KURU	KURU	KURU
29	KURU	0.022	1.00	0.450	-----	1.00	0.340	0.105	0.105	KURU	KURU	KURU
30	KURU	0.002	0.580	0.450	-----	1.00	0.340	0.105	0.105	KURU	KURU	KURU
31	KURU	-----	2.20	0.450	-----	1.00	-----	0.105	-----	KURU	KURU	-----
Maks.	KURU	4.20	8.60	5.50	12.0	9.60	0.850	0.340	0.105	0.053	KURU	KURU
Min.	KURU	KURU	KURU	0.250	0.450	0.850	0.250	0.105	0.053	KURU	KURU	KURU
Ortalama	KURU	0.076	0.198	0.490	1.30	1.45	0.542	0.205	0.105	0.027	KURU	KURU
LT/SN/Km2	0.000	2.93	7.64	18.9	50.1	56.1	20.9	7.89	4.05	1.03	0.000	0.000
AKIM mm.	0.000	7.59	20.5	50.6	121.	150.	54.2	21.1	10.5	2.77	0.000	0.000
MİL. M3	0.000	0.197	0.531	1.31	3.14	3.90	1.41	0.548	0.272	0.072	0.000	0.000

SU YILI (2006) YILLIK TOPLAM AKIM 11.38 MİLYON M3 439 MM. 13.9 LT/SN/Km2

04. Kuzey Ege Havzasi

D04A032 TUZLA ÇAYI KORUBAŞİ

YERİ : BEHRAMKALE-KORUBAŞI KÖY YOLUNUN 8. KM SİNDEN SONRA SAĞA DÖNÜLÜR,3. KM DEKI KÖPRÜDEDIR

26°17'12" Doğu - 39°31'31" Kuzey

YAĞIŞ ALANI : 312.50 km2 YAKLAŞIK KOT : 75 m

GÖZLEM SÜRESİ : 01.10.1984 - 30.09.2006

ORTALAMA AKIMLAR : Gözlem süresinde 2.334 m3/sn. (19 Yıllık) 2006 Su yılında 5.402 m3/sn.

ANLIK EN ÇOK VE EN AZ AKIMLAR:

2006 Su yılında anlık ençok akım	:	445.	m3/sn	25.11.2005
2006 Su yılında anlık enaz akım	:	0.000	m3/sn	01.10.2005
Gözlem süresinde anlık ençok akım	:	590.	m3/sn	01.01.1986
Gözlem süresinde anlık enaz akım	:	0.000	m3/sn	01.10.1985

6. Anahtar Eğrisi (Seviyeler cm olarak)

Seviye	Akım	Seviye	Akım	Seviye	Akım	Seviye	Akım
1	0.002	16	0.400	120	37.0	280	206.
4	0.027	19	0.590	150	61.0	350	290.
7	0.079	30	1.6	190	100.	600	620.
10	0.158	60	7.3	220	131.	700	750.
13	0.270	90	18.5	250	167.		

Akımlar 01 Ekim 2005 'den 30 Eylül 2006' a kadar m3/sn olarak

Gün	Ekim	Kasım	Aralık	Ocak	Şubat	Mart	Nisan	Mayıs	Haziran	Temmuz	Ağustos	Eylül
01	KURU	0.106	3.20	28.8	2.40	6.50	1.90	1.05	0.570	0.160	KURU	KURU
02	0.570	0.080	2.50	14.0	2.30	5.20	1.90	0.965	0.570	0.130	KURU	KURU
03	1.05	0.130	2.10	9.70	2.10	4.90	1.70	0.965	0.570	0.130	KURU	KURU
04	0.440	0.130	1.80	10.5	2.00	4.10	1.70	0.880	0.570	0.106	KURU	KURU
05	0.235	0.130	1.70	6.80	1.90	3.70	1.60	0.880	0.500	0.080	KURU	KURU
06	0.160	0.130	1.60	7.40	35.6	3.40	1.55	0.880	0.500	0.060	KURU	KURU
07	0.106	0.130	1.55	5.20	11.0	65.5	1.50	0.880	0.500	0.106	KURU	KURU
08	0.080	0.130	1.50	4.10	7.00	82.0	1.50	0.965	0.500	0.130	KURU	KURU
09	0.060	0.130	2.10	3.40	5.60	25.2	1.55	1.10	0.640	0.106	KURU	KURU
10	0.044	0.130	1.60	2.90	8.40	21.8	1.50	0.880	0.710	0.060	KURU	KURU
11	0.044	0.130	1.55	2.60	8.40	18.4	1.40	0.880	0.710	0.060	KURU	KURU
12	0.044	0.130	1.40	2.60	6.00	66.4	1.30	0.780	0.640	0.060	KURU	KURU
13	0.044	0.130	1.40	2.40	4.40	78.0	1.30	0.880	0.640	0.060	KURU	KURU
14	0.060	0.160	1.40	2.10	3.90	53.8	1.30	0.880	0.640	0.060	KURU	KURU
15	0.060	0.160	1.55	2.00	3.40	26.4	1.50	0.780	0.640	0.031	KURU	KURU
16	0.060	0.160	1.55	1.90	3.20	21.3	1.30	0.780	0.640	0.021	KURU	KURU
17	0.060	0.235	1.70	1.80	3.10	13.5	1.25	0.710	0.570	0.021	KURU	KURU
18	0.060	0.710	3.40	1.70	2.90	16.0	1.25	0.710	0.500	0.031	KURU	KURU
19	0.080	1.05	25.2	2.40	2.90	13.5	1.15	0.710	0.440	0.031	KURU	KURU
20	0.080	1.15	4.90	6.20	3.10	9.30	1.15	0.710	0.380	0.060	KURU	KURU
21	0.106	0.965	3.20	3.20	3.10	7.40	1.15	0.710	0.380	0.031	KURU	KURU
22	0.106	0.640	2.80	2.80	2.80	6.20	1.10	0.640	0.330	0.009	KURU	KURU
23	0.106	0.780	2.50	3.40	2.60	5.20	1.10	0.640	0.330	0.009	KURU	KURU
24	0.080	176.	2.30	2.60	2.40	4.90	1.05	0.640	0.280	0.004	KURU	KURU
25	0.080	196.	2.00	2.50	33.5	4.20	1.05	0.640	0.235	0.004	KURU	KURU
26	0.080	32.8	1.90	2.50	16.5	3.40	1.05	0.640	0.195	0.002	KURU	KURU
27	0.106	32.8	9.30	2.10	11.0	3.10	0.965	0.570	0.195	0.002	KURU	KURU
28	0.106	29.4	22.4	2.00	7.70	2.90	1.05	0.570	0.160	0.002	KURU	KURU
29	0.106	14.0	138.	1.90	-----	2.50	1.05	0.570	0.160	KURU	KURU	0.440
30	0.106	7.70	60.2	1.90	-----	2.40	1.05	0.570	0.195	KURU	KURU	1.90
31	0.106	-----	153.	2.10	-----	2.30	-----	0.570	-----	KURU	KURU	-----
Maks.	2.80	445.	349.	46.6	105.	315.	2.60	1.60	0.780	0.160	KURU	18.4
Min.	KURU	0.080	1.40	1.70	1.70	2.10	0.965	0.500	0.080	KURU	KURU	KURU
Ortalama	0.143	16.5	14.9	4.69	7.11	18.8	1.33	0.775	0.463	0.051	KURU	0.078
LT/SN/Km2	0.457	52.9	47.6	15.0	22.8	60.2	4.26	2.48	1.48	0.162	0.000	0.250
AKIM mm.	1.22	137.	128.	40.2	55.1	161.	11.0	6.64	3.84	0.433	0.000	0.647
MİL. M3	0.382	42.9	39.9	12.6	17.2	50.4	3.45	2.08	1.20	0.135	0.000	0.202

SU YILI (2006) YILLIK TOPLAM AKIM 170.45 MİLYON M3 545 MM. 17.3 LT/SN/Km2

04. Kuzey Ege Havzasi

D04A036 ZEYTİNLI ÇAYI ZEYTİNLI

YERİ : EDREMİT-ZEYTINLI KASABASINDAKI MESIRE YERININ 300 M KUZEYINDEDIR.
26°57'11" Doğu - 39°37'1" Kuzey

YAĞIŞ ALANI : 123.40 km2 YAKLAŞIK KOT : 35 m

GÖZLEM SÜRESİ : 25.10.1988 - 30.09.2006

ORTALAMA AKIMLAR : Gözlem süresinde 2.893 m3/sn. (16 Yıllık) 2006 Su yılında 5.579 m3/sn.

ANLIK EN ÇOK VE EN AZ AKIMLAR:

2006 Su yılında anlık ençok akım	:	228.	m3/sn	25.11.2005
2006 Su yılında anlık enaz akım	:	0.030	m3/sn	28.10.2005
Gözlem süresinde anlık ençok akım	:	228.	m3/sn	25.11.2005
Gözlem süresinde anlık enaz akım	:	0.000	m3/sn	01.10.1988

9. Anahtar Eğrisi (Seviyeler cm olarak)

Seviye	Akım	Seviye	Akım	Seviye	Akım	Seviye	Akım
35	0.030	90	3.2	160	31.0	202	62.6
46	0.120	100	5.4	170	38.0	250	100.
62	0.520	110	8.0	172	39.6	300	150.
70	0.940	120	11.3	180	46.0	400	250.
80	1.9	135	18.0	200	60.0	440	290.

Akımlar 01 Ekim 2005 'den 30 Eylül 2006' a kadar m3/sn olarak

Gün	Ekim	Kasım	Aralık	Ocak	Şubat	Mart	Nisan	Mayıs	Haziran	Temmuz	Ağustos	Eylül
01	0.067	0.060	6.73	28.4	3.40	22.0	6.73	1.85	0.716	0.190	0.090	0.082
02	0.060	0.120	5.07	20.5	3.40	17.5	6.13	1.73	0.652	0.190	0.090	0.082
03	0.182	0.210	4.60	18.5	3.20	41.0	5.87	1.73	0.652	0.175	0.090	0.082
04	0.060	0.182	4.00	18.5	3.20	25.1	5.60	1.73	0.588	0.175	0.090	0.082
05	0.054	0.167	3.60	15.0	3.20	19.5	5.33	1.62	0.588	0.160	0.082	0.082
06	0.048	0.210	3.40	13.8	8.05	16.6	4.80	1.62	0.588	0.160	0.082	0.082
07	0.048	0.100	3.40	12.0	5.60	36.6	4.60	1.62	0.524	0.160	0.082	0.082
08	0.054	0.167	4.80	10.4	4.80	34.8	5.87	1.50	0.524	0.148	0.082	0.082
09	0.036	0.295	4.40	9.37	4.40	24.6	5.07	1.50	0.524	0.148	0.082	0.082
10	0.036	0.295	3.60	8.38	12.3	19.5	4.40	1.50	0.460	0.135	0.082	0.082
11	0.060	0.351	3.40	7.39	9.70	29.5	4.00	1.40	0.460	0.123	0.082	0.082
12	0.060	0.267	3.40	6.73	7.72	41.0	4.00	1.30	0.428	0.123	0.082	0.082
13	0.060	0.110	3.40	6.13	6.73	31.3	4.00	1.30	0.428	0.110	0.082	0.082
14	0.060	0.151	3.20	5.60	6.13	27.2	3.80	1.20	0.396	0.110	0.082	0.082
15	0.060	0.295	3.20	5.07	5.60	22.0	3.40	1.10	0.396	0.100	0.082	0.082
16	0.042	0.351	3.20	4.80	5.07	19.0	3.20	1.10	0.396	0.100	0.082	0.082
17	0.048	0.678	3.20	4.80	5.07	16.2	3.03	1.04	0.364	0.100	0.082	0.082
18	0.070	1.61	30.7	4.80	5.33	14.6	2.87	1.04	0.332	0.100	0.082	0.082
19	0.070	0.940	18.5	10.4	6.13	13.0	2.87	0.972	0.332	0.100	0.082	0.082
20	0.070	1.23	11.0	9.04	13.0	11.7	3.03	0.972	0.300	0.100	0.082	0.190
21	0.060	0.678	8.05	7.39	10.0	10.7	2.87	0.908	0.300	0.100	0.082	0.460
22	0.054	0.464	6.40	6.73	9.04	10.0	2.53	0.908	0.278	0.100	0.082	1.40
23	0.054	0.464	5.33	6.13	8.38	9.70	2.37	0.908	0.278	0.100	0.082	1.20
24	0.054	53.0	4.60	5.60	8.38	15.4	2.20	0.908	0.256	0.100	0.082	2.20
25	0.054	106.	4.00	5.07	48.3	12.0	2.20	0.844	0.256	0.100	0.082	3.20
26	0.054	31.3	3.80	4.60	48.3	10.4	2.08	0.844	0.256	0.100	0.082	1.97
27	0.042	37.2	10.4	4.40	27.8	9.37	1.97	0.844	0.234	0.100	0.082	1.85
28	0.030	20.0	44.2	4.20	21.0	8.71	1.85	0.780	0.234	0.090	0.082	2.37
29	0.080	13.0	88.1	4.00	-----	8.05	1.97	0.780	0.212	0.090	0.082	6.40
30	0.167	9.04	43.6	3.80	-----	8.05	1.85	0.780	0.212	0.090	0.082	2.20
31	0.136	-----	48.3	3.60	-----	7.39	-----	0.716	-----	0.090	0.082	-----
Maks.	0.940	228.	114.	34.2	73.8	75.4	8.71	1.85	0.716	0.212	0.090	24.6
Min.	0.030	0.060	3.20	3.60	3.03	7.06	1.85	0.716	0.212	0.090	0.082	0.082
Ortalama	0.065	9.30	12.7	8.88	10.8	19.1	3.68	1.19	0.405	0.122	0.083	0.833
LT/SN/Km2	0.531	75.3	103.	71.9	87.8	155.	29.8	9.68	3.29	0.985	0.673	6.75
AKIM mm.	1.42	195.	276.	193.	212.	415.	77.4	25.9	8.52	2.64	1.80	17.5
MİL. M3	0.175	24.1	34.0	23.8	26.2	51.2	9.55	3.20	1.05	0.325	0.222	2.16

SU YILI (2006) YILLIK TOPLAM AKIM 175.98 MİLYON M3 1426 MM. 45.2 LT/SN/Km2

04. Kuzey Ege Havzasi

D04A039 BEZİRGANLAR ÇAYI KAYSER

YERİ : BAYRAMİÇ-KAYSER(ÜÇYOL) KÖYÜNÜN GÜNEYINDEKI KÖPRÜDEDIR.
26°41'11" Doğu - 39°54'8" Kuzey

YAĞIŞ ALANI : 85.68 km2 YAKLAŞIK KOT : 140 m

GÖZLEM SÜRESİ : 26.12.1997 - 30.09.2006

ORTALAMA AKIMLAR : Gözlem süresinde 0.426 m3/sn. (3 Yıllık) 2006 Su yılında 0.534 m3/sn.

ANLIK EN ÇOK VE EN AZ AKIMLAR:

2006 Su yılında anlık ençok akım	:	96.0	m3/sn	18.12.2005
2006 Su yılında anlık enaz akım	:	0.000	m3/sn	01.10.2005
Gözlem süresinde anlık ençok akım	:	292.	m3/sn	16.02.2005
Gözlem süresinde anlık enaz akım	:	0.000	m3/sn	01.10.2003

Akımlar 01 Ekim 2005 'den 30 Eylül 2006' a kadar m3/sn olarak

Gün	Ekim	Kasım	Aralık	Ocak	Şubat	Mart	Nisan	Mayıs	Haziran	Temmuz	Ağustos	Eylül
01	KURU	KURU	0.066	0.800	1.75	0.980	0.210	0.019	KURU	KURU	KURU	KURU
02	KURU	KURU	0.066	0.369	2.54	0.673	0.190	0.012	KURU	KURU	KURU	KURU
03	KURU	KURU	0.050	0.240	2.18	2.18	0.190	0.035	KURU	KURU	KURU	KURU
04	KURU	KURU	0.050	0.190	1.70	1.15	0.167	0.012	KURU	KURU	KURU	KURU
05	KURU	KURU	0.050	0.143	1.53	0.767	0.167	0.012	KURU	KURU	KURU	KURU
06	KURU	KURU	0.066	0.210	7.07	0.560	0.143	0.012	KURU	KURU	KURU	KURU
07	KURU	KURU	0.050	0.143	2.68	2.60	0.143	0.019	KURU	KURU	KURU	KURU
08	KURU	KURU	0.050	0.102	2.54	11.8	0.167	0.006	KURU	KURU	KURU	KURU
09	KURU	KURU	0.038	0.102	2.36	2.60	0.143	0.006	KURU	KURU	KURU	KURU
10	KURU	KURU	0.038	0.084	10.4	1.53	0.120	0.012	KURU	KURU	KURU	KURU
11	KURU	KURU	0.026	0.084	22.8	1.85	0.120	0.006	KURU	KURU	KURU	KURU
12	KURU	KURU	0.026	0.120	6.25	3.00	0.120	0.083	KURU	KURU	KURU	KURU
13	KURU	KURU	0.015	0.530	2.30	3.51	0.102	0.240	KURU	KURU	KURU	KURU
14	KURU	KURU	0.015	0.317	1.23	5.62	0.102	0.035	KURU	KURU	KURU	KURU
15	KURU	KURU	0.015	0.317	0.820	3.32	0.102	0.019	0.006	KURU	KURU	KURU
16	KURU	KURU	0.026	0.421	0.733	2.68	0.084	0.006	0.006	KURU	KURU	KURU
17	KURU	KURU	0.026	0.317	1.15	1.62	0.084	KURU	KURU	KURU	KURU	KURU
18	KURU	KURU	0.850	0.240	3.08	3.51	0.066	KURU	KURU	KURU	KURU	KURU
19	KURU	KURU	1.90	0.820	1.90	3.72	0.066	0.006	KURU	KURU	KURU	KURU
20	KURU	KURU	0.560	1.66	1.41	1.75	0.084	KURU	KURU	KURU	KURU	KURU
21	KURU	KURU	0.294	0.767	0.980	1.19	0.167	KURU	KURU	KURU	KURU	KURU
22	KURU	KURU	0.190	0.500	0.767	0.880	0.133	KURU	KURU	KURU	KURU	KURU
23	KURU	KURU	0.143	2.54	0.620	0.700	0.116	KURU	KURU	KURU	KURU	KURU
24	KURU	0.343	0.120	1.19	0.560	0.620	0.099	KURU	KURU	KURU	KURU	KURU
25	KURU	2.30	0.120	0.850	4.35	0.560	0.083	KURU	KURU	KURU	KURU	KURU
26	KURU	4.45	0.102	0.850	5.10	0.474	0.070	KURU	KURU	KURU	KURU	KURU
27	KURU	2.12	0.102	0.767	2.92	0.421	0.056	KURU	KURU	KURU	KURU	KURU
28	KURU	0.850	0.167	0.733	1.49	0.369	0.045	KURU	KURU	KURU	KURU	KURU
29	KURU	0.190	0.294	0.767	-----	0.317	0.035	KURU	KURU	KURU	KURU	KURU
30	KURU	0.102	0.294	0.850	-----	0.294	0.026	KURU	KURU	KURU	KURU	KURU
31	KURU	-----	1.80	1.23	-----	0.270	-----	KURU	-----	KURU	KURU	-----
Maks.	KURU	15.0	96.0	8.44	53.9	72.5	0.270	5.79	0.006	KURU	KURU	KURU
Min.	KURU	KURU	0.015	0.084	0.530	0.240	0.026	KURU	KURU	KURU	KURU	KURU
Ortalama	KURU	0.345	0.245	0.589	3.33	1.98	0.113	0.017	0.000	KURU	KURU	KURU
LT/SN/Km2	0.000	4.03	2.86	6.87	38.9	23.2	1.32	0.203	0.005	0.000	0.000	0.000
AKIM mm.	0.000	10.4	7.67	18.4	94.0	62.0	3.43	0.545	0.012	0.000	0.000	0.000
MİL. M3	0.000	0.895	0.657	1.58	8.05	5.31	0.294	0.047	0.001	0.000	0.000	0.000

SU YILI (2006) YILLIK TOPLAM AKIM 16.83 MİLYON M3 196 MM. 6.2 LT/SN/Km2

04. Kuzey Ege Havzasi

D04A043 ÇANDERE KINIK

YERİ : KINIK İLÇE MERKEZİNİN BÜYÜKOBA EIMALIKÖY YOLUNA SAPILIR 3 KM SONRA KARAYOLU KÖPRÜSÜNDEDİR
(PAFTA J18)
28°12'27" Doğu - 38°25'19" Kuzey

YAĞIŞ ALANI : 69,20 km2 YAKLAŞIK KOT : 120 m

GÖZLEM SÜRESİ : 05.12.2000 – 30.09.2006

ORTALAMA AKIMLAR : Gözlem süresinde 0.278 m3/sn. (5 Yıllık) 2006 Su yılında 0.290 m3/sn.

ANLIK EN ÇOK VE EN AZ AKIMLAR:

2006 Su yılında anlık ençok akım	:	21.1	m3/sn	10.02.2006
2006 Su yılında anlık enaz akım	:	0.000	m3/sn	05.10.2005
Gözlem süresinde anlık ençok akım	:	37.0	m3/sn	29.01.2004
Gözlem süresinde anlık enaz akım	:	0.000	m3/sn	01.10.2001

4. Anahtar Eğrisi (Seviyeler cm olarak)

Akımlar 01 Ekim 2005 'den 30 Eylül 2006' a kadar m3/sn olarak

Gün	Ekim	Kasım	Aralık	Ocak	Şubat	Mart	Nisan	Mayıs	Haziran	Temmuz	Ağustos	Eylül
01	KURU	0.032	0.305	0.683	0.734	0.512	0.204	0.110	0.030	0.005	0.002	KURU
02	KURU	0.032	0.280	0.512	0.734	0.433	0.179	0.110	0.030	0.005	0.002	KURU
03	KURU	0.032	0.280	0.433	0.734	0.631	0.179	0.074	0.030	0.005	0.002	KURU
04	KURU	0.032	0.280	0.393	0.796	0.472	0.153	0.040	0.030	0.005	0.001	KURU
05	KURU	0.032	0.254	0.334	1.04	0.393	0.153	0.040	0.030	0.005	0.001	KURU
06	0.010	0.032	0.254	0.393	6.81	0.334	0.153	0.040	0.030	0.005	KURU	KURU
07	0.010	0.032	0.254	0.512	2.42	0.552	0.153	0.040	0.030	0.005	0.001	KURU
08	0.010	0.032	0.280	0.433	1.35	2.42	0.153	0.040	0.030	0.005	0.001	KURU
09	0.010	0.032	0.472	0.364	1.10	1.23	0.128	0.040	0.030	0.005	0.002	KURU
10	0.010	0.040	0.305	0.364	7.89	0.734	0.128	0.040	0.030	0.005	KURU	KURU
11	0.010	0.040	0.254	0.334	5.10	0.980	0.128	0.040	0.030	0.005	KURU	KURU
12	0.010	0.040	0.254	0.305	2.55	2.21	0.128	0.040	0.030	0.005	KURU	KURU
13	0.010	0.040	0.229	0.280	1.35	2.55	0.128	0.040	0.030	0.005	KURU	KURU
14	0.010	0.040	0.229	0.280	0.980	1.99	0.128	0.040	0.030	0.005	KURU	KURU
15	0.010	0.040	0.280	0.280	0.631	1.23	0.128	0.040	0.030	0.005	KURU	KURU
16	0.017	0.040	0.433	0.254	0.512	0.919	0.128	0.040	0.001	0.005	KURU	KURU
17	0.017	0.059	0.552	0.254	0.472	0.631	0.128	0.040	0.002	0.005	KURU	KURU
18	0.017	0.177	0.393	0.229	0.472	0.796	0.128	0.040	0.002	0.005	KURU	KURU
19	0.017	0.093	1.29	0.280	0.433	0.683	0.128	0.040	0.002	0.005	KURU	KURU
20	0.017	0.177	0.591	1.10	0.393	0.552	0.128	0.040	0.002	0.005	KURU	KURU
21	0.017	0.109	0.393	0.734	0.433	0.512	0.128	0.040	0.005	0.005	KURU	KURU
22	0.017	0.093	0.334	0.683	0.364	0.472	0.128	0.030	0.005	0.005	KURU	KURU
23	0.017	0.093	0.334	1.67	0.364	0.393	0.128	0.030	0.005	0.005	KURU	KURU
24	0.017	0.093	0.305	0.980	0.280	0.552	0.128	0.030	0.005	0.005	KURU	KURU
25	0.017	0.449	0.280	0.857	0.683	0.472	0.128	0.030	0.005	0.002	KURU	KURU
26	0.017	0.633	0.254	0.857	0.980	0.364	0.128	0.030	0.005	0.002	KURU	KURU
27	0.017	1.89	0.254	0.734	0.734	0.305	0.128	0.030	0.005	0.002	KURU	KURU
28	0.023	0.631	0.254	0.683	0.591	0.254	0.128	0.030	0.005	0.002	KURU	KURU
29	0.023	0.433	0.280	0.683	-----	0.254	0.128	0.030	0.005	0.002	KURU	KURU
30	0.023	0.364	0.280	0.683	-----	0.229	0.110	0.030	0.005	0.002	KURU	KURU
31	0.032	-----	0.683	0.683	-----	0.204	-----	0.030	-----	0.002	KURU	-----
Maks.	0.032	4.43	2.82	2.69	21.1	6.00	0.204	0.110	0.204	0.005	0.002	KURU
Min.	KURU	0.032	0.229	0.204	0.280	0.204	0.110	0.030	KURU	0.002	KURU	KURU
Ortalama	0.013	0.195	0.359	0.557	1.46	0.783	0.138	0.042	0.017	0.004	0.000	KURU
LT/SN/Km2	0.189	2.82	5.18	8.05	21.1	11.3	1.99	0.613	0.245	0.062	0.006	0.000
AKIM mm.	0.506	7.32	13.9	21.6	51.1	30.3	5.15	1.64	0.636	0.167	0.015	0.000
MİL. M3	0.035	0.506	0.961	1.49	3.54	2.10	0.356	0.114	0.044	0.012	0.001	0.000

SU YILI (2006) YILLIK TOPLAM AKIM 9.16 MİLYON M3 132 MM. 4.2 LT/SN/Km2

04. Kuzey Ege Havzasi

D04A045 HİMMETDERE ÇITTAK

YERİ : ALİAĞA ÇITTAK KÖY YOLUNDAN ÇITTAK KÖYÜNE VARILIR. YAKLAŞIK 2 KM İLERİDE DERE ÜZERİNDEDİR
(PAFTA K18 A4)
27°4'10" Doğu - 38°45'12" Kuzey

YAĞIŞ ALANI : 7,40 km2 YAKLAŞIK KOT : 170 m

GÖZLEM SÜRESİ : 06.12.2000 - 30.09.2006

ORTALAMA AKIMLAR : Gözlem süresinde 0.054 m3/sn. (4 Yıllık) 2006 Su yılında 0.046 m3/sn.

ANLIK EN ÇOK VE EN AZ AKIMLAR:

2006 Su yılında anlık ençok akım	:	6.08	m3/sn	11.03.2006
2006 Su yılında anlık enaz akım	:	0.000	m3/sn	01.10.2005
Gözlem süresinde anlık ençok akım	:	6.81	m3/sn	16.11.2004
Gözlem süresinde anlık enaz akım	:	0.000	m3/sn	16.05.2003

İstasyon için kullanılmış anahtar bulunamadı.

Akımlar 01 Ekim 2005 'den 30 Eylül 2006' a kadar m3/sn olarak

Gün	Ekim	Kasım	Aralık	Ocak	Şubat	Mart	Nisan	Mayıs	Haziran	Temmuz	Ağustos	Eylül
01	KURU	KURU	0.001	0.001	0.030	0.112	0.072	0.005	0.005	0.001	0.001	0.001
02	KURU	KURU	0.001	0.001	0.030	0.112	0.051	0.005	0.005	0.001	0.001	0.001
03	KURU	KURU	0.001	0.001	0.030	0.112	0.072	0.005	0.005	0.001	0.001	0.001
04	KURU	KURU	0.001	0.001	0.030	0.072	0.072	0.005	0.005	0.001	0.001	0.001
05	KURU	KURU	0.001	0.001	0.051	0.072	0.051	0.005	0.005	0.001	0.001	0.001
06	KURU	KURU	0.001	0.001	1.00	0.072	0.051	0.005	0.005	0.001	0.001	0.001
07	KURU	KURU	0.001	0.001	0.322	0.483	0.051	0.005	0.005	0.001	0.001	0.001
08	KURU	KURU	0.001	0.001	0.191	1.12	0.051	0.005	0.005	0.001	0.001	0.001
09	KURU	KURU	0.001	0.001	0.191	0.322	0.030	0.005	0.005	0.001	0.001	0.001
10	KURU	KURU	0.001	0.001	1.23	0.191	0.030	0.005	0.005	0.001	0.001	0.001
11	KURU	KURU	0.001	0.001	0.674	0.322	0.030	0.018	0.005	0.001	0.001	0.001
12	KURU	KURU	0.001	0.001	0.578	0.387	0.030	0.018	0.005	0.001	0.001	0.001
13	KURU	KURU	0.001	0.001	0.257	1.00	0.030	0.018	0.005	0.001	0.001	0.001
14	KURU	KURU	0.001	0.001	0.151	1.35	0.030	0.005	0.005	0.001	0.001	0.001
15	KURU	KURU	0.001	0.001	0.112	0.387	0.030	0.005	0.005	0.001	0.001	0.001
16	KURU	KURU	0.001	0.001	0.112	0.191	0.030	0.005	0.005	0.001	0.001	0.001
17	KURU	KURU	0.001	0.001	0.112	0.112	0.030	0.005	0.005	0.001	0.001	0.001
18	KURU	0.005	0.001	0.001	0.072	0.322	0.030	0.005	0.005	0.001	0.001	0.001
19	KURU	0.001	0.018	0.001	0.072	0.191	0.030	0.005	0.005	0.001	0.001	0.001
20	KURU	KURU	0.005	0.001	0.072	0.151	0.030	0.005	0.005	0.001	0.001	0.001
21	KURU	KURU	0.005	0.001	0.072	0.151	0.018	0.005	0.005	0.001	0.001	0.001
22	KURU	KURU	0.005	0.001	0.051	0.112	0.005	0.005	0.005	0.001	0.001	0.001
23	KURU	0.005	0.005	0.001	0.051	0.112	0.005	0.005	0.005	0.001	0.001	0.001
24	KURU	0.005	0.005	0.018	0.051	0.191	0.005	0.005	0.005	0.001	0.001	0.001
25	KURU	0.072	0.001	0.072	0.151	0.151	0.005	0.005	0.005	0.001	0.001	0.001
26	KURU	0.072	0.001	0.051	0.257	0.112	0.005	0.005	0.005	0.001	0.001	0.001
27	KURU	0.072	0.001	0.051	0.151	0.112	0.005	0.005	0.005	0.001	0.001	0.001
28	KURU	0.018	0.001	0.030	0.112	0.112	0.005	0.005	0.005	0.001	0.001	0.001
29	KURU	0.005	0.001	0.030	-----	0.112	0.005	0.005	0.005	0.001	0.001	0.001
30	KURU	0.005	0.001	0.030	-----	0.112	0.005	0.005	0.005	0.001	0.001	0.001
31	KURU	-----	0.001	0.030	-----	0.112	-----	0.005	-----	0.001	0.001	-----
Maks.	KURU	1.12	0.257	0.322	3.99	6.08	0.387	0.030	0.030	0.001	0.001	0.001
Min.	KURU	KURU	0.001	0.001	0.030	0.072	0.005	0.005	0.001	0.001	0.001	0.001
Ortalama	KURU	0.009	0.002	0.011	0.222	0.273	0.030	0.006	0.005	0.001	0.001	0.001
LT/SN/Km2	0.000	1.17	0.296	1.46	30.0	36.9	4.03	0.846	0.676	0.135	0.135	0.135
AKIM mm.	0.000	3.04	0.794	3.91	72.5	98.9	10.4	2.27	1.75	0.362	0.362	0.350
MİL. M3	0.000	0.022	0.006	0.029	0.537	0.732	0.077	0.017	0.013	0.003	0.003	0.003

SU YILI (2006) YILLIK TOPLAM AKIM 1.44 MİLYON M3 195 MM. 6.2 LT/SN/Km2

04. Kuzey Ege Havzasi

D04A046 AKÇAY AYDINCIK

YERİ : KIRKAĞAÇ SOMA KARAYOLUNUN 6.KM SİNDE SAĞA AYRILAN BAYAT KÖYYOLU AYRIMININ BAYAT KÖYÜNDEN İTİBAREN SAĞA DÖNÜLEN YOLUN 2.KAVŞAĞINDAN SOLA GİRİLİR YAKLAŞIK 1 KM SONRAKİ DERE ÜZERİNDEDİR. (PAFTA J19-C1)

27°45'12" Doğu - 39°11'29" Kuzey

YAĞIŞ ALANI : 48,60 km2 YAKLAŞIK KOT : 248 m

GÖZLEM SÜRESİ : 01.10.2000 - 30.09.2006

ORTALAMA AKIMLAR : Gözlem süresinde 0.023 m3/sn. (6 Yıllık) 2006 Su yılında 0.011 m3/sn.

ANLIK EN ÇOK VE EN AZ AKIMLAR:

2006 Su yılında anlık ençok akım	:	1.65	m3/sn	11.03.2006
2006 Su yılında anlık enaz akım	:	0.000	m3/sn	01.10.2005
Gözlem süresinde anlık ençok akım	:	4.48	m3/sn	14.04.2005
Gözlem süresinde anlık enaz akım	:	0.000	m3/sn	01.10.2000

1. Anahtar Eğrisi (Seviyeler cm olarak)

Seviye	Akım	Seviye	Akım	Seviye	Akım	Seviye	Akım
30	0.000	36	0.010	65	1.2	110	4.0
32	0.000	40	0.160	70	1.5	120	4.8
33	0.001	44	0.300	80	2.0	130	5.6
34	0.002	50	0.560	90	2.6	140	6.5
35	0.006	60	0.980	100	3.3	150	7.4

Akımlar 01 Ekim 2005 'den 30 Eylül 2006' a kadar m3/sn olarak

Gün	Ekim	Kasım	Aralık	Ocak	Şubat	Mart	Nisan	Mayıs	Haziran	Temmuz	Ağustos	Eylül
01	KURU	KURU	KURU	KURU	KURU	0.002	0.006	0.002	0.001	0.006	0.001	0.002
02	KURU	KURU	KURU	KURU	KURU	0.001	0.006	0.002	0.001	0.006	0.001	0.002
03	KURU	KURU	KURU	KURU	0.001	0.002	0.006	0.002	0.001	0.006	0.001	0.002
04	KURU	KURU	KURU	KURU	0.001	0.002	0.006	0.002	0.001	0.006	0.001	0.002
05	KURU	KURU	KURU	KURU	0.002	0.001	0.006	0.006	0.002	0.006	KURU	0.002
06	KURU	KURU	KURU	KURU	0.387	0.001	0.006	0.006	0.002	0.006	KURU	0.002
07	KURU	KURU	KURU	KURU	0.160	0.002	0.006	0.006	0.002	0.006	KURU	0.002
08	KURU	KURU	KURU	KURU	0.006	0.160	0.006	0.006	0.002	0.006	KURU	0.002
09	KURU	KURU	KURU	KURU	0.002	0.006	0.006	0.006	0.006	0.006	KURU	0.002
10	KURU	KURU	KURU	KURU	0.195	0.002	0.006	0.006	0.006	0.006	KURU	0.002
11	KURU	KURU	KURU	KURU	0.517	0.085	0.006	0.006	0.006	0.006	KURU	KURU
12	KURU	KURU	KURU	KURU	0.195	0.387	0.006	0.006	0.006	0.006	KURU	KURU
13	KURU	KURU	KURU	KURU	0.085	0.160	0.002	0.006	0.006	0.006	KURU	KURU
14	KURU	KURU	KURU	KURU	0.002	0.265	0.002	0.006	0.006	0.006	KURU	KURU
15	KURU	KURU	KURU	KURU	0.002	0.085	0.002	0.006	0.006	0.006	KURU	KURU
16	KURU	KURU	KURU	KURU	0.001	0.048	0.002	0.006	0.006	0.006	KURU	KURU
17	KURU	KURU	KURU	KURU	KURU	0.048	0.002	0.002	0.006	0.006	KURU	KURU
18	KURU	KURU	KURU	KURU	0.002	0.010	0.006	0.002	0.002	0.006	KURU	KURU
19	KURU	KURU	KURU	KURU	0.123	0.085	0.006	0.002	0.002	0.006	KURU	KURU
20	KURU	KURU	KURU	KURU	0.048	0.010	0.006	0.002	0.002	0.006	KURU	KURU
21	KURU	KURU	KURU	KURU	0.048	0.010	0.006	0.002	0.006	0.002	KURU	KURU
22	KURU	KURU	KURU	KURU	0.006	0.006	0.006	0.002	0.006	0.002	KURU	KURU
23	KURU	KURU	KURU	KURU	0.002	0.006	0.006	0.002	0.006	0.002	KURU	KURU
24	KURU	KURU	KURU	KURU	0.001	0.006	0.006	0.002	0.006	0.002	KURU	KURU
25	KURU	KURU	KURU	KURU	0.010	0.006	0.002	0.002	0.006	0.002	0.002	KURU
26	KURU	KURU	KURU	KURU	0.123	0.006	0.002	0.002	0.006	0.002	0.002	KURU
27	KURU	KURU	KURU	KURU	0.085	0.006	0.002	0.001	0.006	0.002	0.002	KURU
28	KURU	0.001	KURU	KURU	0.006	0.006	0.002	0.001	0.006	0.002	0.002	KURU
29	KURU	KURU	KURU	KURU	-----	0.006	0.002	0.001	0.006	0.001	0.002	KURU
30	KURU	KURU	KURU	KURU	-----	0.006	0.002	0.001	0.006	0.001	0.002	KURU
31	KURU	-----	KURU	KURU	-----	0.006	-----	0.001	-----	0.001	0.002	-----
Maks.	KURU	0.002	0.560	KURU	1.16	1.65	0.006	0.006	0.006	0.006	0.002	0.002
Min.	KURU	KURU	KURU	KURU	KURU	0.001	0.002	0.001	0.001	0.001	KURU	KURU
Ortalama	KURU	0.000	KURU	KURU	0.072	0.046	0.005	0.003	0.004	0.004	0.001	0.001
LT/SN/Km2	0.000	0.001	0.000	0.000	1.48	0.950	0.093	0.070	0.091	0.092	0.012	0.014
AKIM mm.	0.000	0.002	0.000	0.000	3.57	2.55	0.242	0.187	0.235	0.247	0.032	0.036
MİL. M3	0.000	0.000	0.000	0.000	0.174	0.124	0.012	0.009	0.011	0.012	0.002	0.002

SU YILI (2006) YILLIK TOPLAM AKIM 0.35 MİLYON M3 7 MM. 0.2 LT/SN/Km2

04. Kuzey Ege Havzasi

D04A047 İNÖNÜ ÇAYI INÖNÜ

YERİ : İNÖNÜ KÖYÜNÜN 500 M GÜNEYİNDEKI KARAYOLU KÖPRÜSÜNDEDIR.
27°9'8" Doğu - 39°34'38" Kuzey

YAĞIŞ ALANI : 73.00 km2 YAKLAŞIK KOT : 65 m

GÖZLEM SÜRESİ : 20.09.2001 - 30.09.2006

ORTALAMA AKIMLAR : Gözlem süresinde 0.777 m3/sn. (5 Yıllık) 2006 Su yılında 1.420 m3/sn.

ANLIK EN ÇOK VE EN AZ AKIMLAR:

2006 Su yılında anlık ençok akım	:	24.8	m3/sn	11.02.2006
2006 Su yılında anlık enaz akım	:	0.000	m3/sn	30.09.2006
Gözlem süresinde anlık ençok akım	:	24.8	m3/sn	11.02.2006
Gözlem süresinde anlık enaz akım	:	0.000	m3/sn	30.09.2006

Akımlar 01 Ekim 2005 'den 30 Eylül 2006' a kadar m3/sn olarak

Gün	Ekim	Kasım	Aralık	Ocak	Şubat	Mart	Nisan	Mayıs	Haziran	Temmuz	Ağustos	Eylül
01	0.022	0.043	0.340	3.17	3.83	6.62	1.45	0.820	0.132	0.044	0.020	0.024
02	1.70	0.043	0.275	3.17	3.83	6.13	1.34	0.720	0.132	0.051	0.020	0.015
03	0.165	0.043	0.275	3.17	3.83	7.60	1.34	0.720	0.116	0.065	0.015	0.013
04	0.215	0.043	0.340	3.17	3.83	6.62	1.34	0.720	0.116	0.072	0.013	0.013
05	0.215	0.043	0.340	3.17	3.83	5.89	1.34	0.720	0.116	0.065	0.015	0.011
06	0.215	0.043	0.340	3.17	5.73	5.64	1.34	0.720	0.116	0.051	0.020	0.011
07	0.215	0.076	0.410	3.17	4.17	7.88	1.22	0.720	0.116	0.051	0.017	0.011
08	0.215	0.076	0.635	3.17	3.83	9.45	1.34	0.720	0.132	0.037	0.015	0.009
09	0.215	0.076	0.475	3.17	3.83	3.52	1.22	0.720	0.180	0.030	0.015	0.015
10	0.215	0.120	0.410	3.17	8.83	3.01	1.22	0.720	0.164	0.030	0.015	0.017
11	0.215	0.120	0.410	3.17	13.9	2.84	1.22	0.720	0.132	0.037	0.015	0.017
12	0.215	0.120	0.410	3.17	9.20	2.84	1.22	0.720	0.132	0.051	0.013	0.030
13	0.215	0.120	0.475	3.17	8.15	2.84	1.22	0.720	0.148	0.072	0.017	0.024
14	0.215	0.120	0.475	3.17	7.60	3.01	1.22	0.720	0.148	0.079	0.015	0.020
15	0.215	0.120	0.475	3.17	7.11	2.84	1.22	0.720	0.132	0.065	0.015	0.024
16	0.215	0.120	0.550	3.17	6.62	2.84	1.22	0.720	0.148	0.072	0.011	0.020
17	0.215	0.165	0.475	3.17	6.38	2.50	1.22	0.720	0.116	0.065	0.013	0.024
18	0.215	0.275	0.550	3.17	7.36	2.67	1.22	0.720	0.093	0.058	0.020	0.026
19	0.165	0.275	1.02	7.67	7.88	2.67	1.22	0.720	0.079	0.051	0.015	0.030
20	0.165	0.720	0.920	5.73	8.43	2.50	1.22	0.720	0.072	0.037	0.015	0.026
21	0.120	0.215	0.720	4.17	8.15	2.36	1.22	0.720	0.058	0.030	0.009	0.030
22	0.120	0.215	0.720	3.83	7.88	2.23	1.22	0.720	0.058	0.037	0.015	0.044
23	0.076	0.215	0.635	3.83	7.36	2.09	1.22	0.720	0.058	0.044	0.011	0.058
24	0.076	1.82	0.635	3.83	7.36	1.96	1.22	0.720	0.058	0.044	0.004	0.132
25	0.076	2.36	0.550	3.83	10.2	1.96	1.22	0.720	0.051	0.030	0.005	0.096
26	0.043	1.57	0.550	3.83	10.2	1.82	1.22	0.720	0.051	0.022	0.007	0.096
27	0.043	1.34	0.475	3.83	8.43	1.82	0.920	0.180	0.051	0.024	0.013	0.065
28	0.043	0.820	0.475	3.83	7.11	1.70	0.720	0.180	0.051	0.026	0.011	0.065
29	0.043	1.12	0.920	3.83	-----	1.70	0.820	0.164	0.058	0.022	0.013	0.974
30	0.043	0.550	0.635	3.83	-----	1.57	0.820	0.148	0.058	0.020	0.015	0.445
31	0.043	-----	1.82	3.83	-----	1.57	-----	0.164	-----	0.013	0.015	-----
Maks.	22.9	6.27	8.64	15.4	24.8	14.7	1.45	0.820	0.196	0.079	0.026	0.974
Min.	0.022	0.043	0.275	3.17	3.83	1.45	0.720	0.148	0.044	0.006	0.004	KURU
Ortalama	0.199	0.433	0.572	3.64	6.96	3.57	1.20	0.634	0.102	0.045	0.014	0.079
LT/SN/Km2	2.73	5.93	7.84	49.9	95.3	48.9	16.4	8.69	1.40	0.616	0.191	1.09
AKIM mm.	7.30	15.4	21.0	134.	231.	131.	42.5	23.3	3.64	1.65	0.511	2.82
MİL. M3	0.533	1.12	1.53	9.76	16.8	9.56	3.11	1.70	0.265	0.121	0.037	0.206

SU YILI (2006) YILLIK TOPLAM AKIM 44.74 MİLYON M3 613 MM. 19.5 LT/SN/Km2

04. Kuzey Ege Havzasi

D04A051 CUMALI D. CUMALI

YERİ : KINIK SOMA KAKAYOLUNUN CUMALI KÖY SAPAĞINDAN KÖYE VARILIR.İSTASYON CUMALI KÖYÜNÜN İÇİNDEKİ KÖPRÜDEDİR.(PAFTA J18-C2-C3)
27°28'45" Doğu - 39°8'10" Kuzey

YAĞIŞ ALANI : 84,50 km2 YAKLAŞIK KOT : 115 m

GÖZLEM SÜRESİ : 01.10.2002 - 30.09.2006

ORTALAMA AKIMLAR : Gözlem süresinde 0.198 m3/sn. (4 Yıllık) 2006 Su yılında 0.096 m3/sn.

ANLIK EN ÇOK VE EN AZ AKIMLAR:

2006 Su yılında anlık ençok akım	:	1.95	m3/sn	24.09.2006
2006 Su yılında anlık enaz akım	:	0.014	m3/sn	14.12.2005
Gözlem süresinde anlık ençok akım	:	3.04	m3/sn	11.11.2002
Gözlem süresinde anlık enaz akım	:	0.000	m3/sn	13.08.2004

6. Anahtar Eğrisi (Seviyeler cm olarak)

Seviye	Akım	Seviye	Akım	Seviye	Akım	Seviye	Akım
1	0.210	17	0.908	33	1.5	90	4.2
4	0.405	20	1.0	37	1.6	130	6.6
7	0.541	23	1.1	40	1.8	140	7.3
10	0.656	27	1.3	43	1.9	150	8.0
13	0.769	30	1.4	50	2.2		

Akımlar 01 Ekim 2005 'den 30 Eylül 2006' a kadar m3/sn olarak

Gün	Ekim	Kasım	Aralık	Ocak	Şubat	Mart	Nisan	Mayıs	Haziran	Temmuz	Ağustos	Eylül
01	0.218	0.045	0.045	0.062	0.183	0.079	0.300	0.125	0.079	0.034	0.045	0.062
02	0.183	0.045	0.045	0.062	0.183	0.079	0.183	0.183	0.079	0.034	0.062	0.062
03	0.183	0.045	0.045	0.034	0.183	0.062	0.218	0.183	0.062	0.034	0.045	0.062
04	0.183	0.045	0.045	0.034	0.183	0.045	0.259	0.183	0.062	0.034	0.045	0.062
05	0.152	0.045	0.045	0.034	0.183	0.034	0.218	0.152	0.062	0.034	0.062	0.062
06	0.152	0.045	0.045	0.062	0.300	0.034	0.152	0.152	0.062	0.034	0.062	0.079
07	0.125	0.045	0.045	0.101	0.183	0.045	0.183	0.152	0.062	0.034	0.079	0.079
08	0.125	0.045	0.045	0.062	0.183	0.125	0.125	0.152	0.045	0.034	0.079	0.062
09	0.125	0.045	0.045	0.062	0.152	0.152	0.101	0.183	0.045	0.079	0.125	0.062
10	0.125	0.045	0.045	0.062	0.218	0.101	0.062	0.152	0.062	0.062	0.183	0.062
11	0.101	0.045	0.045	0.062	0.183	0.079	0.062	0.152	0.079	0.045	0.125	0.062
12	0.079	0.045	0.045	0.062	0.183	0.125	0.062	0.183	0.079	0.034	0.101	0.062
13	0.152	0.045	0.045	0.062	0.183	0.259	0.079	0.152	0.079	0.034	0.062	0.062
14	0.152	0.045	0.034	0.045	0.183	0.259	0.079	0.101	0.079	0.034	0.062	0.079
15	0.079	0.045	0.022	0.045	0.183	0.218	0.079	0.062	0.125	0.034	0.045	0.079
16	0.079	0.045	0.022	0.045	0.183	0.183	0.101	0.062	0.101	0.034	0.045	0.079
17	0.079	0.045	0.034	0.045	0.183	0.259	0.152	0.079	0.062	0.034	0.045	0.079
18	0.045	0.045	0.034	0.045	0.183	0.183	0.152	0.079	0.045	0.034	0.045	0.101
19	0.045	0.045	0.034	0.062	0.125	0.218	0.152	0.079	0.079	0.034	0.045	0.101
20	0.045	0.045	0.034	0.045	0.152	0.259	0.183	0.079	0.045	0.034	0.045	0.125
21	0.045	0.045	0.034	0.034	0.183	0.183	0.183	0.079	0.045	0.034	0.045	0.079
22	0.045	0.045	0.034	0.034	0.183	0.218	0.218	0.218	0.183	0.034	0.045	0.101
23	0.045	0.045	0.034	0.062	0.183	0.259	0.183	0.079	0.079	0.034	0.062	0.125
24	0.045	0.045	0.045	0.045	0.125	0.259	0.183	0.101	0.062	0.045	0.062	0.183
25	0.045	0.045	0.062	0.045	0.062	0.259	0.259	0.125	0.079	0.034	0.062	0.125
26	0.045	0.045	0.045	0.079	0.101	0.218	0.259	0.101	0.045	0.034	0.062	0.125
27	0.045	0.045	0.079	0.101	0.101	0.152	0.259	0.125	0.034	0.034	0.062	0.125
28	0.045	0.045	0.079	0.125	0.079	0.259	0.218	0.101	0.034	0.034	0.062	0.152
29	0.045	0.045	0.079	0.125	-----	0.218	0.183	0.101	0.034	0.062	0.062	0.439
30	0.045	0.045	0.062	0.125	-----	0.300	0.125	0.101	0.034	0.101	0.062	0.218
31	0.045	-----	0.062	0.152	-----	0.300	-----	0.101	-----	0.045	0.062	-----
Maks.	0.808	0.045	0.101	0.300	0.537	0.439	0.390	0.864	0.488	0.152	0.218	1.95
Min.	0.045	0.045	0.014	0.034	0.045	0.034	0.062	0.062	0.034	0.034	0.034	0.062
Ortalama	0.094	0.045	0.046	0.065	0.168	0.175	0.166	0.125	0.067	0.040	0.066	0.105
LT/SN/Km2	1.12	0.533	0.540	0.771	1.99	2.07	1.96	1.48	0.798	0.479	0.785	1.24
AKIM mm.	2.99	1.38	1.45	2.07	4.81	5.54	5.08	3.96	2.07	1.28	2.10	3.23
MİL. M3	0.252	0.117	0.122	0.175	0.407	0.469	0.430	0.335	0.175	0.108	0.178	0.273

SU YILI (2006) YILLIK TOPLAM AKIM 3.04 MİLYON M3 36 MM. 1.1 LT/SN/Km2

04. Kuzey Ege Havzasi

D04A052 KIŞLA DERESİ DERECBASI

YERİ : HAVRAN İLÇESINE BAĞLI KÖYLÜCE KÖYÜNÜN 3 KM GÜNEYİNDEKİ MEZARLIĞIN İÇİNDEDİR.
27°10'14" Doğu - 39°31'4" Kuzey

YAĞIŞ ALANI : 54.70 km2 YAKLAŞIK KOT : 208 m

GÖZLEM SÜRESİ : 01.10.2005 - 30.09.2006

ORTALAMA AKIMLAR : Gözlem süresinde 0.354 m3/sn. (1 Yıllık) 2006 Su yılında 0.354 m3/sn.

ANLIK EN ÇOK VE EN AZ AKIMLAR:

2006 Su yılında anlık ençok akım	:	26.9	m3/sn	11.02.2006
2006 Su yılında anlık enaz akım	:	0.001	m3/sn	15.07.2006
Gözlem süresinde anlık ençok akım	:	26.9	m3/sn	11.02.2006
Gözlem süresinde anlık enaz akım	:	0.001	m3/sn	15.07.2006

Akımlar 01 Ekim 2005 'den 30 Eylül 2006' a kadar m3/sn olarak

Gün	Ekim	Kasım	Aralık	Ocak	Şubat	Mart	Nisan	Mayıs	Haziran	Temmuz	Ağustos	Eylül
01	0.052	0.031	0.142	0.375	0.270	1.25	0.445	0.165	0.031	0.010	0.002	0.002
02	0.040	0.031	0.142	0.270	0.270	1.02	0.410	0.165	0.040	0.006	0.002	0.002
03	0.040	0.040	0.126	0.212	0.241	2.03	0.375	0.142	0.040	0.010	0.003	0.002
04	0.040	0.040	0.126	0.185	0.241	1.25	0.340	0.142	0.031	0.010	0.002	0.002
05	0.031	0.040	0.126	0.165	0.340	1.02	0.305	0.142	0.024	0.010	0.002	0.002
06	0.031	0.040	0.126	0.165	2.71	0.890	0.270	0.142	0.024	0.010	0.001	0.002
07	0.031	0.040	0.126	0.142	1.32	1.09	0.270	0.126	0.024	0.006	0.001	0.002
08	0.031	0.040	0.142	0.126	0.757	3.64	0.445	0.126	0.080	0.006	0.001	0.001
09	0.031	0.052	0.109	0.126	0.543	2.03	0.375	0.142	0.109	0.006	0.001	0.001
10	0.031	0.063	0.089	0.126	16.3	1.40	0.340	0.126	0.080	0.006	0.001	0.001
11	0.031	0.063	0.089	0.109	10.3	1.32	0.340	0.126	0.063	0.006	0.001	0.001
12	0.024	0.063	0.089	0.109	3.37	1.51	0.305	0.126	0.052	0.006	0.001	0.001
13	0.024	0.063	0.089	0.109	1.93	1.93	0.305	0.126	0.052	0.006	0.001	0.001
14	0.024	0.063	0.089	0.109	1.32	2.35	0.305	0.126	0.052	0.006	0.001	0.001
15	0.024	0.063	0.089	0.089	1.02	1.82	0.305	0.126	0.040	0.003	0.001	0.001
16	0.024	0.063	0.109	0.089	0.823	1.51	0.270	0.126	0.040	0.002	0.001	0.001
17	0.024	0.080	0.126	0.089	0.757	1.25	0.241	0.126	0.040	0.001	0.001	0.001
18	0.024	0.142	0.212	0.109	0.757	1.40	0.241	0.109	0.031	0.001	0.001	0.002
19	0.024	0.165	0.757	1.09	0.690	1.25	0.212	0.109	0.031	0.001	0.001	0.003
20	0.024	0.305	0.375	1.72	0.690	1.02	0.212	0.109	0.016	0.001	0.001	0.006
21	0.024	0.126	0.241	0.690	0.641	0.890	0.212	0.109	0.010	0.001	0.001	0.024
22	0.024	0.080	0.185	0.494	0.592	0.823	0.185	0.109	0.016	0.001	0.001	0.006
23	0.024	0.089	0.165	0.690	0.543	0.757	0.185	0.109	0.016	0.002	0.001	0.006
24	0.024	0.142	0.126	0.494	0.690	0.757	0.185	0.089	0.010	0.002	0.001	0.031
25	0.024	1.61	0.109	0.410	3.24	0.641	0.165	0.080	0.010	0.002	0.001	0.024
26	0.024	0.890	0.109	0.340	2.58	0.592	0.165	0.063	0.010	0.002	0.001	0.016
27	0.024	0.494	0.109	0.305	2.14	0.543	0.142	0.063	0.010	0.002	0.001	0.016
28	0.024	0.305	0.109	0.270	1.51	0.494	0.142	0.052	0.010	0.002	0.001	0.024
29	0.024	0.305	0.165	0.241	-----	0.445	0.165	0.052	0.010	0.002	0.001	0.031
30	0.024	0.212	0.126	0.241	-----	0.494	0.165	0.040	0.010	0.002	0.001	0.024
31	0.031	-----	0.592	0.241	-----	0.494	-----	0.031	-----	0.002	0.002	-----
Maks.	0.052	11.6	4.30	10.7	26.9	12.3	0.957	0.185	0.543	0.016	0.016	1.02
Min.	0.024	0.031	0.089	0.080	0.241	0.410	0.142	0.016	0.006	0.001	0.001	0.001
Ortalama	0.028	0.191	0.171	0.320	2.02	1.22	0.267	0.110	0.034	0.004	0.001	0.008
LT/SN/Km2	0.517	3.50	3.13	5.86	36.9	22.4	4.89	2.02	0.617	0.078	0.022	0.144
AKIM mm.	1.38	9.07	8.39	15.7	89.4	59.9	12.7	5.41	1.60	0.210	0.060	0.374
MİL. M3	0.076	0.496	0.459	0.858	4.89	3.28	0.693	0.296	0.087	0.011	0.003	0.020

SU YILI (2006) YILLIK TOPLAM AKIM 11.17 MİLYON M3 204 MM. 6.5 LT/SN/Km2

04. Kuzey Ege Havzasi

D04A053 ILICA D. SARICALAR

YERİ : BERGAMA GÖÇBEYLİ SARICALAR KÖYÜNDEN 1 KM. SONRA SOMA'YA GİDEN YOLUN ÜZERİNDEDİR (PAFTAJ18-C2)
27°27'26" Doğu - 39°12'10" Kuzey

YAĞIŞ ALANI : 150,00 km2 YAKLAŞIK KOT : 90 m

GÖZLEM SÜRESİ : 01.10.2005 - 30.09.2006

ORTALAMA AKIMLAR : Gözlem süresinde 1.060 m3/sn. (1 Yıllık) 2006 Su yılında 1.060 m3/sn.

ANLIK EN ÇOK VE EN AZ AKIMLAR:

2006 Su yılında anlık ençok akım	:	139.	m3/sn	11.03.2006
2006 Su yılında anlık enaz akım	:	0.000	m3/sn	23.07.2006
Gözlem süresinde anlık ençok akım	:	139.	m3/sn	11.03.2006
Gözlem süresinde anlık enaz akım	:	0.000	m3/sn	23.07.2006

3. Anahtar Eğrisi (Seviyeler cm olarak)

Seviye	Akım	Seviye	Akım	Seviye	Akım	Seviye	Akım
1	0.000	11	0.001	80	4.4	300	157.
3	0.000	15	0.004	100	8.9	400	310.
5	0.000	25	0.033	170	39.4	450	400.
7	0.000	40	0.370	200	65.2	500	496.
9	0.000	60	1.7	250	108.	528	554.

Akımlar 01 Ekim 2005 'den 30 Eylül 2006' a kadar m3/sn olarak

Gün	Ekim	Kasım	Aralık	Ocak	Şubat	Mart	Nisan	Mayıs	Haziran	Temmuz	Ağustos	Eylül
01	0.009	0.016	0.349	3.36	1.44	4.83	1.14	0.540	0.123	0.042	KURU	KURU
02	0.009	0.019	0.214	1.77	1.55	3.53	1.14	0.348	0.123	0.024	KURU	KURU
03	0.009	0.021	0.214	1.33	1.55	4.99	1.14	0.348	0.106	0.033	KURU	KURU
04	0.009	0.026	0.113	1.04	1.55	3.19	1.07	0.289	0.089	0.061	KURU	KURU
05	0.009	0.026	0.102	0.954	1.66	2.50	1.07	0.289	0.080	0.038	KURU	KURU
06	0.009	0.026	0.102	1.13	8.93	2.21	1.07	0.289	0.089	0.033	KURU	KURU
07	0.009	0.026	0.102	0.865	4.83	4.99	1.07	0.289	0.089	0.029	KURU	0.004
08	0.009	0.026	0.214	0.776	3.19	17.3	1.07	0.289	0.123	0.024	KURU	0.004
09	0.010	0.031	0.659	0.717	2.35	6.51	1.07	0.289	0.156	0.017	KURU	0.005
10	0.011	0.031	0.164	0.659	8.63	4.68	1.07	0.289	0.139	0.017	KURU	0.005
11	0.014	0.031	0.164	0.600	16.8	13.8	0.993	0.289	0.123	0.017	KURU	0.015
12	0.014	0.031	0.102	0.600	5.91	17.2	0.918	0.231	0.123	0.015	KURU	0.015
13	0.014	0.031	0.102	0.600	4.04	9.52	0.918	0.289	0.123	0.015	KURU	0.015
14	0.016	0.031	0.102	0.542	2.84	8.41	0.918	0.289	0.123	0.015	KURU	0.017
15	0.014	0.031	0.102	0.483	2.21	5.35	0.918	0.231	0.123	0.012	KURU	0.017
16	0.016	0.031	0.102	0.483	1.77	4.20	0.918	0.289	0.139	0.012	KURU	0.017
17	0.016	0.031	0.102	0.483	1.66	3.24	0.842	0.289	0.139	0.007	KURU	0.024
18	0.016	0.113	0.214	0.483	1.92	3.81	0.842	0.289	0.106	0.005	KURU	0.024
19	0.016	0.113	2.50	3.36	2.06	3.24	0.842	0.406	0.089	0.004	KURU	0.029
20	0.016	1.55	0.717	4.37	1.77	2.66	0.842	0.348	0.080	0.001	KURU	0.029
21	0.016	0.214	0.483	1.92	1.55	2.22	0.766	0.289	0.070	KURU	KURU	0.029
22	0.016	0.102	0.214	1.44	1.44	1.97	0.766	0.289	0.051	KURU	KURU	0.029
23	0.016	0.102	0.164	3.36	1.33	1.72	0.766	0.231	0.033	KURU	KURU	0.029
24	0.016	0.164	0.164	2.06	1.33	1.72	0.766	0.173	0.033	KURU	KURU	0.029
25	0.016	8.93	0.113	1.77	14.6	1.60	0.766	0.173	0.029	KURU	KURU	0.029
26	0.016	4.52	0.113	1.44	9.37	1.35	0.766	0.156	0.024	KURU	KURU	0.029
27	0.016	4.37	0.113	1.22	6.82	1.22	0.766	0.156	0.033	KURU	KURU	0.029
28	0.016	1.66	0.214	1.13	4.68	1.14	0.766	0.156	0.038	KURU	KURU	0.038
29	0.016	0.865	3.02	1.04	-----	1.07	0.766	0.173	0.042	KURU	KURU	0.051
30	0.016	0.600	3.19	1.04	-----	1.07	0.766	0.156	0.051	KURU	KURU	0.061
31	0.016	-----	6.51	1.22	-----	1.07	-----	0.139	-----	KURU	KURU	-----
Maks.	0.026	78.0	25.6	19.0	37.4	139.	1.14	1.07	0.231	0.080	KURU	0.070
Min.	0.009	0.016	0.102	0.483	1.22	1.07	0.766	0.139	0.017	KURU	KURU	KURU
Ortalama	0.014	0.792	0.669	1.36	4.21	4.59	0.917	0.268	0.090	0.014	KURU	0.019
LT/SN/Km2	0.091	5.28	4.46	9.08	28.0	30.6	6.12	1.78	0.598	0.091	0.000	0.127
AKIM mm.	0.242	13.7	11.9	24.3	67.8	82.0	15.9	4.78	1.55	0.242	0.000	0.330
MİL. M3	0.036	2.05	1.79	3.65	10.2	12.3	2.38	0.717	0.232	0.036	0.000	0.050

SU YILI (2006) YILLIK TOPLAM AKIM 33.44 MİLYON M3 223 MM. 7.1 LT/SN/Km2

04. Kuzey Ege Havzasi

D04A054 KOCADERE MUSACALI

YERİ : ALİAGADAN ŞAKRANA VARILIR ŞAKRAN YÜKSEKKÖY JANDARMA (DÖRTYOL) YOLUN 22 KM DEN İTİBAREN 10 KM SONRA MARUFLAR KÖYÜNDEN SAĞA SAPILIP 2 KM SONRA DEĞİRMENİN YANINDADIR.(J18-D3) 27°13'47" Doğu - 39°3'24" Kuzey

YAĞIŞ ALANI : 52,30 km2 YAKLAŞIK KOT : 90 m

GÖZLEM SÜRESİ : 01.01.2005 - 30.09.2006

ORTALAMA AKIMLAR : Gözlem süresinde 0.500 m3/sn. (1 Yıllık) 2006 Su yılında 0.500 m3/sn.

ANLIK EN ÇOK VE EN AZ AKIMLAR:

2006 Su yılında anlık ençok akım	:	18.7	m3/sn	06.02.2006
2006 Su yılında anlık enaz akım	:	0.021	m3/sn	01.10.2005
Gözlem süresinde anlık ençok akım	:	18.7	m3/sn	06.02.2006
Gözlem süresinde anlık enaz akım	:	0.021	m3/sn	01.10.2005

1. Anahtar Eğrisi (Seviyeler cm olarak)

Seviye	Akım	Seviye	Akım	Seviye	Akım	Seviye	Akım
1	0.000	13	0.056	60	6.4	160	30.8
3	0.000	18	0.221	80	10.3	180	37.0
5	0.000	22	0.398	100	14.6	200	43.2
7	0.005	30	1.1	120	19.4	240	57.5
9	0.014	40	2.6	140	24.6	250	61.1

Akımlar 01 Ekim 2005 'den 30 Eylül 2006' a kadar m3/sn olarak

Gün	Ekim	Kasım	Aralık	Ocak	Şubat	Mart	Nisan	Mayıs	Haziran	Temmuz	Ağustos	Eylül
01	0.021	0.085	0.149	1.33	1.01	0.149	0.746	0.746	0.133	0.073	0.053	0.053
02	0.021	0.085	0.149	0.820	1.25	0.085	0.746	0.746	0.133	0.073	0.053	0.053
03	0.021	0.085	0.149	0.673	1.25	0.596	0.746	0.304	0.133	0.073	0.053	0.053
04	0.021	0.085	0.149	0.599	1.25	0.221	0.746	0.133	0.133	0.073	0.053	0.053
05	0.021	0.085	0.149	0.526	1.95	0.113	0.746	0.133	0.133	0.073	0.053	0.053
06	0.021	0.085	0.149	0.802	8.95	0.044	0.746	0.133	0.133	0.073	0.053	0.053
07	0.021	0.085	0.149	0.398	2.77	0.802	0.746	0.133	0.133	0.073	0.053	0.053
08	0.021	0.085	0.307	0.264	1.79	5.86	0.746	0.133	0.133	0.073	0.053	0.053
09	0.021	0.085	0.530	0.185	1.79	0.802	0.746	0.133	0.133	0.073	0.053	0.053
10	0.021	0.085	0.264	0.185	8.18	0.596	0.746	0.133	0.133	0.073	0.053	0.053
11	0.021	0.085	0.221	0.185	6.05	2.26	0.746	0.133	0.133	0.073	0.053	0.053
12	0.021	0.085	0.221	0.185	3.55	3.93	0.746	0.133	0.133	0.073	0.053	0.053
13	0.021	0.085	0.221	0.185	1.65	4.70	0.746	0.133	0.133	0.073	0.053	0.053
14	0.021	0.085	0.221	0.185	1.38	3.16	0.746	0.133	0.073	0.073	0.053	0.053
15	0.021	0.085	0.221	0.185	1.25	1.95	0.746	0.133	0.073	0.073	0.053	0.053
16	0.021	0.085	0.699	0.185	1.25	1.25	0.746	0.133	0.073	0.073	0.053	0.053
17	0.021	0.085	0.802	0.113	1.25	0.904	0.746	0.133	0.073	0.073	0.053	0.053
18	0.044	0.221	0.398	0.113	1.25	1.95	0.746	0.133	0.073	0.073	0.053	0.053
19	0.085	0.221	2.26	0.353	1.25	1.71	0.746	0.133	0.073	0.073	0.053	0.053
20	0.085	0.307	0.746	1.79	1.11	1.22	0.746	0.133	0.073	0.073	0.053	0.053
21	0.085	0.221	0.526	0.699	1.11	0.893	0.746	0.133	0.073	0.073	0.053	0.053
22	0.085	0.221	0.470	0.464	1.11	0.820	0.746	0.133	0.073	0.073	0.053	0.053
23	0.085	0.221	0.415	2.77	1.11	0.820	0.746	0.133	0.073	0.073	0.053	0.053
24	0.085	0.221	0.415	0.904	0.530	0.820	0.746	0.133	0.073	0.073	0.053	0.053
25	0.085	1.25	0.415	0.904	1.01	0.820	0.746	0.133	0.073	0.073	0.053	0.053
26	0.085	1.79	0.415	0.904	1.38	0.820	0.746	0.133	0.073	0.073	0.053	0.053
27	0.085	3.74	0.415	0.802	0.464	0.820	0.746	0.133	0.073	0.073	0.053	0.053
28	0.085	0.530	0.415	0.699	0.221	0.746	0.746	0.133	0.073	0.073	0.053	0.053
29	0.085	0.264	0.599	0.596	-----	0.746	0.746	0.133	0.073	0.073	0.053	0.053
30	0.085	0.185	0.470	0.596	-----	0.746	0.746	0.133	0.073	0.053	0.053	0.053
31	0.085	-----	3.30	0.904	-----	0.746	-----	0.133	-----	0.053	0.053	-----
Maks.	0.113	8.18	12.0	5.67	18.7	13.3	0.746	1.84	0.166	0.073	0.073	0.053
Min.	0.021	0.085	0.149	0.113	0.085	0.044	0.746	0.133	0.073	0.053	0.053	0.053
Ortalama	0.049	0.361	0.516	0.629	2.04	1.33	0.746	0.178	0.099	0.072	0.053	0.053
LT/SN/Km2	0.929	6.91	9.87	12.0	39.0	25.3	14.3	3.40	1.89	1.37	1.01	1.01
AKIM mm.	2.49	17.9	26.4	32.2	94.4	67.9	37.0	9.12	4.91	3.67	2.71	2.63
MİL. M3	0.130	0.936	1.38	1.69	4.93	3.55	1.93	0.477	0.257	0.192	0.142	0.137

SU YILI (2006) YILLIK TOPLAM AKIM 15.75 MİLYON M3 301 MM. 9.6 LT/SN/Km2

05

GEDİZ HAVZASI

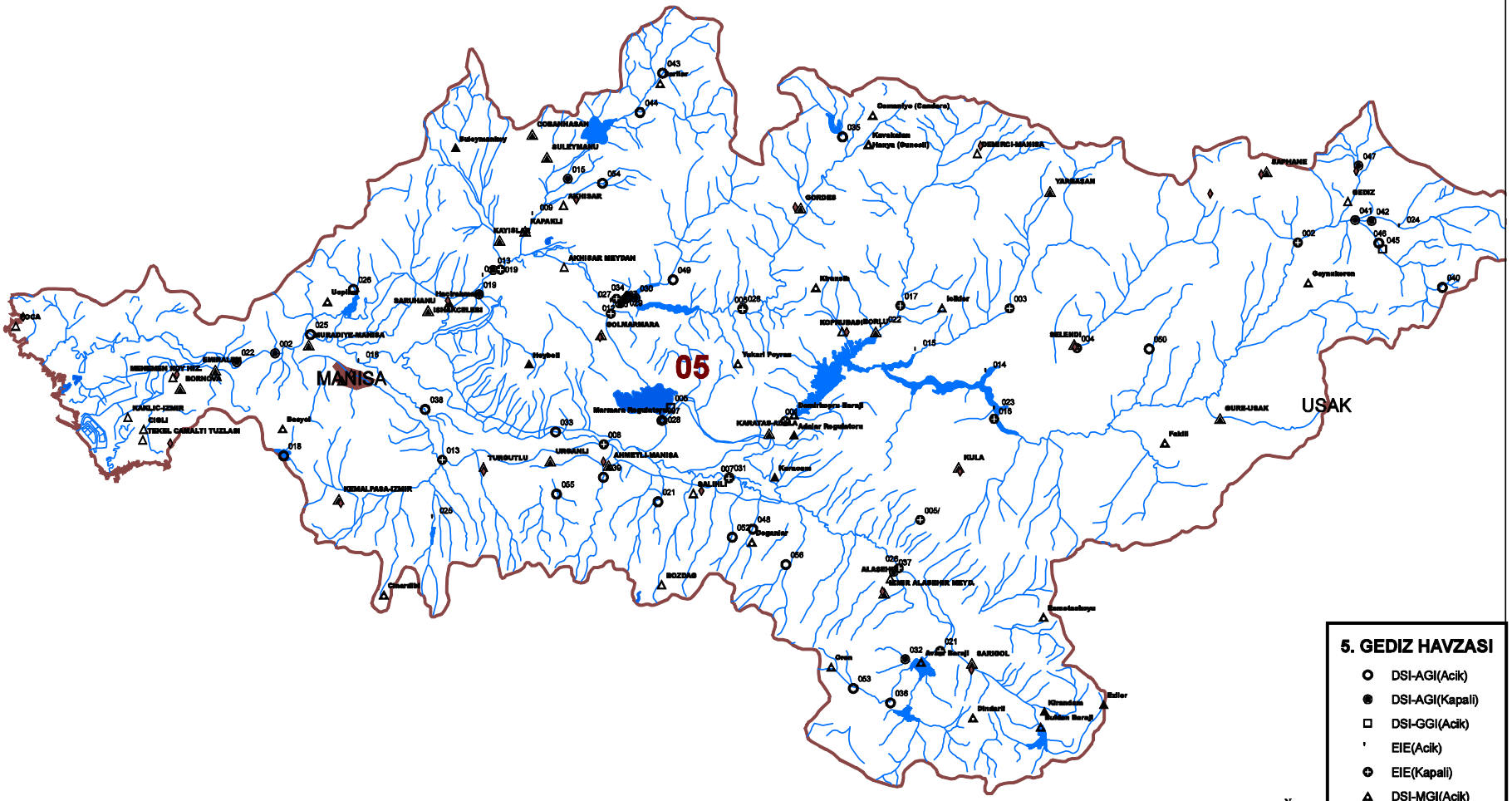
05
MANISA
USAK
Gediz Barajı
Adaler Regulatörü
Marmara Gölü
Demirköprü Barajı
Kulam Barajı
Arslar Barajı
5. GEDIZ HAVZASI
DSI-AGI(Acik)
DSI-AGI(Kapali)
DSI-GGI(Acik)
EIE(Acik)
EIE(Kapali)
DSI-MGI(Acik)
DSI-MGI(Kapali)
DMI-MGI(Acik)
DMI-MGI(Kapali)
N
1:650.761

05. Gediz Havzasi

D05A018 NİF Ç. ÇİCEKLİ

YERİ : İZMİR MANİSA YOLUNUN 8.KM SİNDEN SAĞA AYRILAN KÖY YOLUNUN 2.KM SİNDEKİ ÇİÇEKLİ KÖYÜNE VARILIR. MANSABA DOĞRU 2,5.KM SİNDEN SAĞA AYRILAN ORMAN YOLUNUN 1,5.KM SİNDEDİR.(PAFTA L18-C4) 27°17'54" Doğu - 38°29'41" Kuzey

YAĞIŞ ALANI : 39,50 km2 **YAKLAŞIK KOT** : 276 m

GÖZLEM SÜRESİ : 03.06.1968 - 30.09.2006

ORTALAMA AKIMLAR : Gözlem süresinde 0.243 m3/sn. (36 Yıllık) 2006 Su yılında 0.199 m3/sn.

ANLIK EN ÇOK VE EN AZ AKIMLAR:

2006 Su yılında anlık ençok akım	:	48.0	m3/sn	10.02.2006
2006 Su yılında anlık enaz akım	:	0.000	m3/sn	01.10.2005
Gözlem süresinde anlık ençok akım	:	91.0	m3/sn	15.12.1981
Gözlem süresinde anlık enaz akım	:	0.000	m3/sn	01.10.1968

3. Anahtar Eğrisi (Seviyeler cm olarak)

Seviye	Akım	Seviye	Akım	Seviye	Akım	Seviye	Akım
1	0.000	25	1.8	90	20.9	170	57.4
4	0.001	33	3.5	110	29.5	180	62.1
7	0.014	45	6.2	140	43.3	190	66.8
10	0.085	60	10.3	150	48.0	200	71.5
17	0.591	75	15.3	160	52.7		

Akımlar 01 Ekim 2005 'den 30 Eylül 2006' a kadar m3/sn olarak

Gün	Ekim	Kasım	Aralık	Ocak	Şubat	Mart	Nisan	Mayıs	Haziran	Temmuz	Ağustos	Eylül
01	KURU	KURU	0.008	0.085	0.053	0.291	0.188	0.063	KURU	KURU	KURU	KURU
02	KURU	KURU	0.008	0.014	0.053	0.154	0.188	0.063	KURU	KURU	KURU	KURU
03	KURU	KURU	0.008	0.007	0.154	0.085	0.188	0.063	KURU	KURU	KURU	KURU
04	KURU	KURU	0.008	0.003	0.085	0.085	0.188	0.063	KURU	KURU	KURU	KURU
05	KURU	KURU	0.001	0.003	0.366	0.053	0.188	0.063	KURU	KURU	KURU	KURU
06	KURU	KURU	KURU	0.053	4.59	0.030	0.188	0.063	KURU	KURU	KURU	KURU
07	KURU	KURU	KURU	1.96	0.516	0.222	0.188	0.063	KURU	KURU	KURU	KURU
08	KURU	KURU	KURU	0.154	0.222	5.24	0.119	0.063	KURU	KURU	KURU	KURU
09	KURU	KURU	KURU	0.030	0.154	1.40	0.119	0.029	KURU	KURU	KURU	KURU
10	KURU	KURU	KURU	0.030	10.9	0.642	0.119	0.029	KURU	KURU	KURU	KURU
11	KURU	KURU	KURU	0.014	4.59	0.642	0.119	0.029	KURU	KURU	KURU	KURU
12	KURU	KURU	KURU	0.014	1.32	2.26	0.119	0.029	KURU	KURU	KURU	KURU
13	KURU	KURU	KURU	0.007	0.441	2.74	0.119	0.029	KURU	KURU	KURU	KURU
14	KURU	KURU	KURU	0.007	0.222	1.96	0.119	0.008	KURU	KURU	KURU	KURU
15	KURU	KURU	KURU	0.003	0.085	1.54	0.063	0.008	KURU	KURU	KURU	KURU
16	KURU	KURU	KURU	0.001	0.053	1.06	0.063	0.008	KURU	KURU	KURU	KURU
17	KURU	KURU	KURU	0.001	0.053	0.736	0.063	0.008	KURU	KURU	KURU	KURU
18	KURU	KURU	KURU	0.001	0.030	1.54	0.063	0.008	KURU	KURU	KURU	KURU
19	KURU	0.063	0.642	0.007	0.030	1.40	0.063	0.008	KURU	KURU	KURU	KURU
20	KURU	0.277	0.188	0.222	0.030	0.736	0.063	0.001	KURU	KURU	KURU	KURU
21	KURU	0.029	0.063	0.030	0.030	0.642	0.063	0.001	KURU	KURU	KURU	KURU
22	KURU	0.008	0.063	0.085	0.030	0.548	0.063	KURU	KURU	KURU	KURU	KURU
23	KURU	0.008	0.029	1.96	0.030	0.454	0.063	KURU	KURU	KURU	KURU	KURU
24	KURU	0.008	0.008	0.366	0.030	0.360	0.063	KURU	KURU	KURU	KURU	KURU
25	KURU	0.277	0.008	0.085	1.80	0.360	0.063	KURU	KURU	KURU	KURU	KURU
26	KURU	0.736	0.008	0.030	2.58	0.360	0.063	KURU	KURU	KURU	KURU	KURU
27	KURU	1.40	0.008	0.030	0.516	0.360	0.063	KURU	KURU	KURU	KURU	KURU
28	KURU	0.277	0.008	0.014	0.291	0.277	0.063	KURU	KURU	KURU	KURU	KURU
29	KURU	0.063	0.008	0.014	-----	0.277	0.063	KURU	KURU	KURU	KURU	0.360
30	KURU	0.029	0.188	0.014	-----	0.188	0.063	KURU	KURU	KURU	KURU	0.001
31	KURU	-----	2.58	0.030	-----	0.188	-----	KURU	-----	KURU	KURU	-----
Maks.	KURU	2.42	6.46	4.59	48.0	6.72	0.188	0.063	KURU	KURU	KURU	0.548
Min.	KURU	KURU	KURU	0.001	0.030	0.030	0.063	KURU	KURU	KURU	KURU	KURU
Ortalama	KURU	0.106	0.124	0.170	1.04	0.865	0.105	0.023	KURU	KURU	KURU	0.012
LT/SN/Km2	0.000	2.68	3.13	4.31	26.5	21.9	2.66	0.571	0.000	0.000	0.000	0.305
AKIM mm.	0.000	6.94	8.39	11.5	64.0	58.7	6.91	1.53	0.000	0.000	0.000	0.790
MİL. M3	0.000	0.274	0.331	0.456	2.53	2.32	0.273	0.060	0.000	0.000	0.000	0.031

SU YILI (2006) YILLIK TOPLAM AKIM 6.27 MİLYON M3 159 MM. 5.0 LT/SN/Km2

05. Gediz Havzasi

D05A026 SARMA Ç. SARMA

YERİ : **MANİSA ÜÇPINAR BUCAĞI KALE KÖYÜ YOLUNUN 37.KM DEKİ KÖPRÜNÜN MENBAĞINDADIR.(PAFTA K18-C2)**
27°23'58" Doğu - 38°46'10" Kuzey

YAĞIŞ ALANI : **52,30 km2** **YAKLAŞIK KOT : 117 m**

GÖZLEM SÜRESİ : **01.10.1969 - 30.09.2006**

ORTALAMA AKIMLAR : **Gözlem süresinde 0.293 m3/sn. (36 Yıllık) 2006 Su yılında 0.148 m3/sn.**

ANLIK EN ÇOK VE EN AZ AKIMLAR:

2006 Su yılında anlık ençok akım	**:**	**30.4**	**m3/sn**	**13.06.2006**
2006 Su yılında anlık enaz akım	**:**	**0.001**	**m3/sn**	**29.05.2006**
Gözlem süresinde anlık ençok akım	**:**	**91.0**	**m3/sn**	**29.11.1971**
Gözlem süresinde anlık enaz akım	**:**	**0.000**	**m3/sn**	**23.07.1972**

13. Anahtar Eğrisi (Seviyeler cm olarak)

Seviye	Akım	Seviye	Akım	Seviye	Akım	Seviye	Akım
1	0.000	16	0.000	35	0.037	160	14.8
4	0.000	19	0.000	50	0.291	190	23.4
7	0.000	22	0.000	70	1.0	220	34.2
10	0.000	25	0.000	100	3.5	250	46.4
13	0.000	28	0.006	130	8.2	280	59.0

Akımlar 01 Ekim 2005 'den 30 Eylül 2006' a kadar m3/sn olarak

Gün	Ekim	Kasım	Aralık	Ocak	Şubat	Mart	Nisan	Mayıs	Haziran	Temmuz	Ağustos	Eylül
01	0.018	0.022	0.035	0.110	0.207	0.097	0.071	0.020	0.015	0.004	0.003	0.004
02	0.018	0.022	0.028	0.035	0.188	0.084	0.071	0.020	0.015	0.004	0.003	0.008
03	0.018	0.022	0.028	0.035	0.188	0.084	0.058	0.015	0.015	0.004	0.003	0.008
04	0.018	0.022	0.020	0.035	0.170	0.084	0.058	0.015	0.015	0.004	0.001	0.008
05	0.018	0.018	0.020	0.047	0.170	0.084	0.058	0.015	0.015	0.004	0.001	0.011
06	0.022	0.018	0.020	0.028	0.155	0.071	0.047	0.010	0.015	0.004	0.001	0.011
07	0.022	0.018	0.020	0.028	0.155	0.225	0.047	0.010	0.010	0.004	0.001	0.011
08	0.022	0.018	0.015	0.028	0.170	2.80	0.047	0.010	0.010	0.004	0.001	0.011
09	0.022	0.018	0.028	0.028	0.484	1.08	0.047	0.010	0.010	0.004	0.001	0.011
10	0.022	0.022	0.028	0.028	0.416	0.518	0.035	0.006	0.010	0.004	0.001	0.011
11	0.022	0.022	0.020	0.028	0.348	0.348	0.035	0.006	0.010	0.004	0.001	0.011
12	0.022	0.022	0.020	0.028	0.262	1.08	0.035	0.006	0.010	0.004	0.001	0.011
13	0.022	0.022	0.015	0.028	0.225	1.83	0.035	0.006	5.80	0.004	0.001	0.013
14	0.022	0.022	0.015	0.020	0.207	3.52	0.028	0.006	4.12	0.004	0.001	0.013
15	0.022	0.022	0.035	0.020	0.207	1.83	0.028	0.004	0.521	0.004	0.001	0.013
16	0.022	0.022	0.140	0.020	0.188	0.736	0.028	0.004	0.154	0.004	0.001	0.013
17	0.022	0.033	0.140	0.020	0.188	0.450	0.028	0.004	0.076	0.004	0.001	0.013
18	0.022	0.155	0.110	0.020	0.170	0.262	0.028	0.004	0.055	0.004	0.001	0.013
19	0.018	0.020	0.084	0.028	0.170	0.225	0.028	0.003	0.039	0.004	0.001	0.013
20	0.013	0.015	0.084	0.225	0.155	0.207	0.020	0.003	0.028	0.004	0.001	0.013
21	0.013	0.010	0.071	1.03	0.155	0.188	0.035	0.003	0.033	0.004	0.001	0.013
22	0.013	0.006	0.071	0.552	0.140	0.170	0.035	0.003	0.087	0.003	0.001	0.013
23	0.018	0.006	0.058	0.348	0.155	0.155	0.028	0.003	0.018	0.003	0.001	0.013
24	0.022	0.015	0.058	0.586	0.140	0.155	0.028	0.003	0.018	0.003	0.001	0.097
25	0.022	0.035	0.047	0.262	0.125	0.140	0.028	0.002	0.018	0.003	0.001	0.330
26	0.022	0.348	0.047	3.76	0.110	0.140	0.028	0.002	0.013	0.003	0.001	0.192
27	0.022	0.794	0.035	2.17	0.110	0.125	0.020	0.002	0.013	0.003	0.001	0.116
28	0.022	0.348	0.035	1.20	0.097	0.125	0.020	0.002	0.011	0.003	0.001	0.087
29	0.022	0.170	0.071	0.620	-----	0.110	0.020	0.001	0.008	0.003	0.001	0.076
30	0.022	0.071	0.852	0.348	-----	0.110	0.020	0.001	0.004	0.003	0.001	0.066
31	0.022	-----	0.314	0.348	-----	0.097	-----	0.001	-----	0.003	0.001	-----
Maks.	KURU	1.08	1.55	7.50	0.620	5.50	0.084	0.020	30.4	0.004	0.003	0.404
Min.	KURU	0.006	0.006	0.020	0.097	0.071	0.020	0.001	0.004	0.003	0.001	0.001
Ortalama	0.020	0.079	0.083	0.389	0.195	0.553	0.036	0.006	0.372	0.004	0.001	0.041
LT/SN/Km2	0.387	1.50	1.58	7.44	3.73	10.6	0.697	0.123	7.12	0.070	0.023	0.779
AKIM mm.	1.04	3.90	4.24	19.9	9.01	28.3	1.81	0.330	18.4	0.188	0.061	2.02
MİL. M3	0.054	0.204	0.222	1.04	0.471	1.48	0.095	0.017	0.965	0.010	0.003	0.106

SU YILI (2006) YILLIK TOPLAM AKIM 4.67 MİLYON M3 89 MM. 2.8 LT/SN/Km2

05. Gediz Havzasi

D05A035 INDERESİ GÜNESLİ

YERİ : GÖRDES DEMİRCİLİ YOLUNUN 10.KM.SİNDE SOLA AYRILAN GÜNEŞLİ DARGILI HAM YOLUNUN 8 KM.SİNDE KARAYOLU KÖPRÜSÜNDEDİR. (PAFTA J20-C3)
28°22'0" Doğu - 39°3'17" Kuzey

YAĞIŞ ALANI : 88,00 km2 **YAKLAŞIK KOT** : 598 m

GÖZLEM SÜRESİ : 01.10.1983 - 30.09.2006

ORTALAMA AKIMLAR : Gözlem süresinde 0.573 m3/sn. (18 Yıllık) 2006 Su yılında 0.604 m3/sn.

ANLIK EN ÇOK VE EN AZ AKIMLAR:

2006 Su yılında anlık ençok akım	:	40.5	m3/sn	12.03.2006
2006 Su yılında anlık enaz akım	:	0.000	m3/sn	01.10.2005
Gözlem süresinde anlık ençok akım	:	40.5	m3/sn	12.03.2006
Gözlem süresinde anlık enaz akım	:	0.000	m3/sn	03.08.1985

13. Anahtar Eğrisi (Seviyeler cm olarak)

Seviye	Akım	Seviye	Akım	Seviye	Akım	Seviye	Akım
1	0.000	16	0.001	70	2.9	220	34.0
4	0.000	20	0.004	100	7.2	230	36.5
7	0.000	23	0.009	130	13.5	235	37.8
10	0.000	30	0.056	160	19.8	240	38.0
13	0.000	50	0.830	190	26.5	250	40.5

Akımlar 01 Ekim 2005 'den 30 Eylül 2006' a kadar m3/sn olarak

Gün	Ekim	Kasım	Aralık	Ocak	Şubat	Mart	Nisan	Mayıs	Haziran	Temmuz	Ağustos	Eylül
01	KURU	0.048	0.115	0.618	0.274	2.18	0.671	0.459	0.194	0.012	KURU	KURU
02	KURU	0.048	0.115	0.274	0.274	1.42	0.671	0.406	0.194	0.009	KURU	KURU
03	KURU	0.048	0.115	0.221	0.353	4.00	0.618	0.406	0.194	0.009	KURU	KURU
04	KURU	0.048	0.115	0.221	0.406	1.97	0.565	0.406	0.194	0.007	KURU	KURU
05	KURU	0.048	0.088	0.221	0.459	1.31	0.565	0.406	0.194	0.007	KURU	KURU
06	0.031	0.048	0.088	0.274	6.58	0.923	0.565	0.406	0.194	0.005	KURU	KURU
07	0.031	0.048	0.088	0.221	2.92	1.31	0.512	0.406	0.194	0.005	KURU	KURU
08	0.031	0.048	0.088	0.221	1.53	3.16	0.512	0.406	0.141	0.005	KURU	KURU
09	0.031	0.048	0.115	0.194	0.923	1.64	0.512	0.406	0.141	0.007	KURU	KURU
10	0.031	0.072	0.115	0.194	4.12	1.86	0.512	0.406	0.141	0.007	KURU	KURU
11	0.031	0.072	0.115	0.194	17.9	2.92	0.512	0.406	0.141	0.004	KURU	KURU
12	0.031	0.072	0.115	0.194	4.43	19.0	0.512	0.406	0.115	0.004	KURU	KURU
13	0.031	0.072	0.115	0.194	2.39	6.12	0.512	0.353	0.115	0.004	KURU	KURU
14	0.031	0.072	0.115	0.194	1.53	9.72	0.512	0.300	0.115	0.004	KURU	KURU
15	0.031	0.072	0.115	0.168	1.02	5.34	0.512	0.221	0.115	0.004	KURU	KURU
16	0.031	0.072	0.115	0.168	0.724	3.88	0.512	0.247	0.088	0.002	KURU	KURU
17	0.031	0.072	0.194	0.168	0.671	3.16	0.512	0.274	0.088	0.003	KURU	KURU
18	0.031	0.221	0.459	0.168	2.28	2.81	0.512	0.274	0.088	0.002	KURU	KURU
19	0.031	0.088	3.40	2.92	2.07	2.39	0.459	0.274	0.088	0.002	KURU	KURU
20	0.031	0.194	0.459	2.39	2.07	2.07	0.459	0.247	0.088	0.003	KURU	KURU
21	0.031	0.088	0.247	0.671	1.75	1.75	0.459	0.247	0.048	0.004	KURU	KURU
22	0.031	0.088	0.194	0.512	1.53	1.53	0.459	0.247	0.048	0.004	KURU	KURU
23	0.031	0.088	0.194	1.02	1.31	1.31	0.459	0.194	0.048	0.004	KURU	KURU
24	0.031	0.088	0.194	0.565	1.11	1.42	0.459	0.194	0.031	0.003	KURU	KURU
25	0.031	0.141	0.168	0.459	4.43	1.31	0.459	0.194	0.031	0.003	KURU	KURU
26	0.031	1.64	0.168	0.406	4.12	1.11	0.459	0.194	0.031	0.003	KURU	KURU
27	0.031	0.671	0.194	0.353	2.92	0.923	0.459	0.194	0.023	0.002	KURU	KURU
28	0.048	0.194	0.194	0.274	1.97	0.830	0.459	0.194	0.015	0.002	KURU	KURU
29	0.048	0.115	0.247	0.274	-----	0.830	0.459	0.194	0.015	0.002	KURU	KURU
30	0.048	0.115	0.194	0.274	-----	1.11	0.459	0.194	0.012	0.001	KURU	KURU
31	0.048	-----	1.86	0.221	-----	0.923	-----	0.194	-----	KURU	KURU	-----
Maks.	0.141	7.20	12.2	23.8	31.0	40.5	0.671	0.459	0.194	0.012	KURU	KURU
Min.	KURU	0.048	0.072	0.072	0.221	0.724	0.459	0.194	0.012	KURU	KURU	KURU
Ortalama	0.028	0.158	0.326	0.466	2.57	2.91	0.510	0.302	0.104	0.004	KURU	KURU
LT/SN/Km2	0.320	1.80	3.70	5.30	29.2	33.1	5.80	3.43	1.18	0.049	0.000	0.000
AKIM mm.	0.858	4.65	9.91	14.2	70.8	88.6	15.0	9.18	3.07	0.131	0.000	0.000
MİL. M3	0.076	0.409	0.872	1.25	6.23	7.80	1.32	0.808	0.270	0.011	0.000	0.000

SU YILI (2006) YILLIK TOPLAM AKIM 19.05 MİLYON M3 216 MM. 6.9 LT/SN/Km2

05. Gediz Havzasi

D05A039 AHMETLİ Ç. DEREKÖY

YERİ : **MANİSA AHMETLİ KARAYOLUNUN HİMMETLER DEREKÖY AYRIMININ 25.KM SİNDEKİ KARAYOLU KÖPRÜSÜNÜN 50 M MEMBAĞINDADIR. L19 B2**
27°56'33" Doğu - 38°29'36" Kuzey

YAĞIŞ ALANI : **95,00 km2** **YAKLAŞIK KOT : 125 m**

GÖZLEM SÜRESİ : **01.10.1987 - 30.09.2006**

ORTALAMA AKIMLAR : **Gözlem süresinde 0.633 m3/sn. (18 Yıllık) 2006 Su yılında 0.867 m3/sn.**

ANLIK EN ÇOK VE EN AZ AKIMLAR:

2006 Su yılında anlık ençok akım	**:**	**29.0**	**m3/sn**	**19.01.2006**
2006 Su yılında anlık enaz akım	**:**	**0.025**	**m3/sn**	**17.07.2006**
Gözlem süresinde anlık ençok akım	**:**	**56.0**	**m3/sn**	**30.01.2004**
Gözlem süresinde anlık enaz akım	**:**	**0.000**	**m3/sn**	**22.08.2000**

6. Anahtar Eğrisi (Seviyeler cm olarak)

Seviye	Akım	Seviye	Akım	Seviye	Akım	Seviye	Akım
1	0.033	16	0.235	100	8.2	250	47.0
4	0.052	19	0.310	130	13.0	260	50.0
7	0.080	30	0.750	170	23.0	270	53.0
10	0.118	44	1.8	210	35.0	280	56.0
13	0.170	70	4.6	240	44.0		

Akımlar 01 Ekim 2005 'den 30 Eylül 2006' a kadar m3/sn olarak

Gün	Ekim	Kasım	Aralık	Ocak	Şubat	Mart	Nisan	Mayıs	Haziran	Temmuz	Ağustos	Eylül
01	0.092	0.189	0.326	1.06	1.01	1.65	1.06	0.569	0.197	0.057	0.025	0.057
02	0.092	0.189	0.287	1.01	1.01	1.46	1.01	0.569	0.197	0.057	0.025	0.045
03	0.111	0.189	0.287	0.896	1.06	1.46	0.951	0.514	0.197	0.057	0.025	0.045
04	0.111	0.189	0.287	0.787	1.13	1.39	0.896	0.479	0.197	0.057	0.025	0.045
05	0.111	0.189	0.287	0.787	1.72	1.32	0.896	0.444	0.197	0.045	0.025	0.045
06	0.111	0.189	0.287	1.06	9.28	1.26	0.842	0.444	0.197	0.045	0.025	0.045
07	0.111	0.189	0.287	1.39	4.28	1.65	0.842	0.410	0.166	0.045	0.025	0.045
08	0.111	0.189	0.287	1.52	2.85	7.18	0.842	0.410	0.166	0.045	0.025	0.045
09	0.111	0.189	0.254	1.19	2.68	4.08	0.842	0.375	0.166	0.034	0.025	0.045
10	0.135	0.189	0.254	0.951	11.2	2.85	0.787	0.375	0.166	0.034	0.025	0.045
11	0.135	0.159	0.254	0.733	20.6	2.76	0.787	0.375	0.145	0.034	0.025	0.045
12	0.135	0.159	0.254	0.787	4.91	7.86	0.787	0.340	0.145	0.034	0.025	0.045
13	0.135	0.159	0.254	0.733	3.12	9.28	0.732	0.340	0.283	0.034	0.025	0.045
14	0.135	0.159	0.254	0.678	2.85	7.18	0.732	0.311	0.226	0.034	0.025	0.045
15	0.135	0.159	0.287	0.623	2.76	4.91	0.678	0.283	0.166	0.034	0.025	0.045
16	0.135	0.159	0.287	0.623	2.59	3.68	0.678	0.254	0.166	0.034	0.025	0.045
17	0.135	0.222	0.287	0.569	2.50	2.85	0.678	0.254	0.124	0.025	0.025	0.045
18	0.135	0.896	0.569	0.569	2.42	2.85	0.678	0.226	0.124	0.025	0.025	0.045
19	0.135	0.514	3.68	5.23	2.34	2.50	0.678	0.226	0.124	0.025	0.025	0.045
20	0.135	0.623	1.65	6.50	2.34	2.27	0.623	0.197	0.124	0.025	0.025	0.045
21	0.135	0.326	1.39	2.34	2.27	2.19	0.623	0.197	0.103	0.025	0.025	0.045
22	0.159	0.287	1.32	1.80	2.27	2.03	0.623	0.197	0.103	0.025	0.025	0.045
23	0.159	0.326	1.26	2.19	2.19	1.88	0.623	0.197	0.085	0.025	0.025	0.045
24	0.159	0.366	1.26	2.19	2.19	1.72	0.623	0.197	0.085	0.025	0.025	0.057
25	0.159	1.06	1.26	2.11	2.11	1.59	0.569	0.197	0.085	0.025	0.025	0.145
26	0.159	3.48	1.19	1.95	2.03	1.46	0.569	0.197	0.070	0.025	0.025	0.145
27	0.159	1.72	1.19	1.65	1.95	1.39	0.569	0.197	0.070	0.025	0.025	0.145
28	0.159	0.787	1.19	1.39	1.88	1.32	0.569	0.197	0.057	0.025	0.034	0.166
29	0.159	0.405	1.39	1.19	-----	1.26	0.514	0.197	0.057	0.025	0.034	0.311
30	0.159	0.366	1.26	1.06	-----	1.19	0.514	0.197	0.057	0.025	0.034	0.197
31	0.189	-----	1.13	1.01	-----	1.13	-----	0.197	-----	0.025	0.045	-----
Maks.	0.189	4.38	5.44	29.0	29.0	12.0	1.06	0.569	0.283	0.057	0.057	0.375
Min.	0.092	0.159	0.254	0.514	1.01	1.06	0.514	0.197	0.057	0.025	0.025	0.045
Ortalama	0.136	0.474	0.789	1.50	3.56	2.83	0.727	0.308	0.142	0.034	0.027	0.074
LT/SN/Km2	1.43	4.99	8.31	15.8	37.4	29.7	7.65	3.25	1.49	0.358	0.279	0.776
AKIM mm.	3.82	12.9	22.2	42.4	90.5	79.7	19.8	8.70	3.86	0.959	0.748	2.01
MİL. M3	0.363	1.23	2.11	4.02	8.60	7.57	1.88	0.826	0.367	0.091	0.071	0.191

SU YILI (2006) YILLIK TOPLAM AKIM 27.32 MİLYON M3 288 MM. 9.1 LT/SN/Km2

05. Gediz Havzasi

D05A043 CEMAL D. KAYGANLI

YERİ : **AKHİSAR SINDIRGI DEVLET KARAYOLUNUN 27.KM.SINDEKI KÖPRÜDEDIR. J20-D4**
28°0'19" Doğu - 39°7'30" Kuzey

YAĞIŞ ALANI : **64,00 km2** **YAKLAŞIK KOT : 290 m**

GÖZLEM SÜRESİ : **01.10.1990 - 30.09.2006**

ORTALAMA AKIMLAR : **Gözlem süresinde 0.431 m3/sn. (15 Yıllık) 2006 Su yılında 0.592 m3/sn.**

ANLIK EN ÇOK VE EN AZ AKIMLAR:

2006 Su yılında anlık ençok akım	**:**	**16.7**	**m3/sn**	**06.02.2006**
2006 Su yılında anlık enaz akım	**:**	**0.000**	**m3/sn**	**05.08.2006**
Gözlem süresinde anlık ençok akım	**:**	**23.0**	**m3/sn**	**22.12.2001**
Gözlem süresinde anlık enaz akım	**:**	**0.000**	**m3/sn**	**13.08.1991**

4. Anahtar Eğrisi (Seviyeler cm olarak)

Seviye	Akım	Seviye	Akım	Seviye	Akım	Seviye	Akım
1	0.000	16	0.002	45	0.696	90	7.0
4	0.000	20	0.008	60	1.9	120	11.7
7	0.000	25	0.060	75	4.0	150	17.1
10	0.000	29	0.131	80	5.0	175	22.1
13	0.001	35	0.284	85	5.8	210	29.6

Akımlar 01 Ekim 2005 'den 30 Eylül 2006' a kadar m3/sn olarak

Gün	Ekim	Kasım	Aralık	Ocak	Şubat	Mart	Nisan	Mayıs	Haziran	Temmuz	Ağustos	Eylül
01	0.008	0.052	0.131	0.596	0.757	2.02	0.646	0.284	0.070	0.019	0.004	KURU
02	0.008	0.052	0.131	0.446	0.878	1.85	0.646	0.284	0.070	0.019	0.004	KURU
03	0.008	0.304	0.131	0.370	0.818	2.50	0.596	0.258	0.070	0.019	0.004	KURU
04	0.008	0.304	0.131	0.332	0.939	2.21	0.596	0.258	0.070	0.019	0.003	KURU
05	0.008	0.272	0.112	0.308	1.72	1.71	0.596	0.258	0.070	0.019	KURU	KURU
06	0.008	0.240	0.112	0.308	13.5	1.49	0.546	0.258	0.070	0.019	KURU	KURU
07	0.008	0.240	0.112	0.284	4.20	1.49	0.496	0.258	0.070	0.019	KURU	KURU
08	0.008	0.240	0.112	0.258	2.15	2.50	0.496	0.258	0.080	0.019	KURU	KURU
09	0.008	0.240	0.205	0.258	1.91	2.77	0.496	0.232	0.284	0.019	KURU	KURU
10	0.008	0.240	0.153	0.232	4.00	2.31	0.496	0.232	0.153	0.019	KURU	KURU
11	0.008	0.240	0.112	0.205	9.05	2.31	0.446	0.232	0.080	0.014	KURU	KURU
12	0.008	0.240	0.112	0.205	5.33	7.18	0.446	0.232	0.080	0.014	KURU	KURU
13	0.008	0.232	0.112	0.205	3.67	5.16	0.446	0.205	0.080	0.008	KURU	KURU
14	0.008	0.153	0.112	0.179	2.26	6.31	0.446	0.205	0.080	0.006	KURU	KURU
15	0.008	0.112	0.112	0.179	1.81	3.51	0.446	0.205	0.070	0.006	KURU	KURU
16	0.008	0.112	1.17	0.179	1.53	2.64	0.446	0.205	0.070	0.004	KURU	KURU
17	0.052	0.112	0.646	0.179	1.43	2.26	0.408	0.205	0.070	0.004	KURU	KURU
18	0.208	0.131	0.408	0.179	4.39	2.91	0.370	0.205	0.070	0.004	KURU	KURU
19	0.035	0.131	1.43	0.284	4.39	2.15	0.370	0.205	0.070	0.004	KURU	KURU
20	0.008	0.131	0.596	1.34	4.00	1.62	0.370	0.205	0.070	0.004	KURU	0.001
21	0.008	0.153	0.408	0.878	3.04	1.43	0.370	0.205	0.070	0.004	KURU	0.001
22	0.008	0.205	0.332	0.939	2.91	1.34	0.370	0.153	0.070	0.004	KURU	0.001
23	0.008	0.232	0.308	0.646	2.21	1.17	0.370	0.112	0.070	0.004	KURU	0.002
24	0.008	0.232	0.284	0.696	2.21	1.00	0.370	0.112	0.040	0.004	KURU	0.008
25	0.008	0.284	0.258	0.696	5.66	1.00	0.332	0.112	0.030	0.004	KURU	0.008
26	0.008	0.179	0.258	0.696	5.49	1.00	0.308	0.080	0.019	0.004	KURU	0.008
27	0.008	0.179	0.370	0.646	3.04	0.939	0.284	0.080	0.019	0.004	KURU	0.004
28	0.008	0.179	0.496	0.646	2.31	0.818	0.284	0.080	0.019	0.004	KURU	0.006
29	0.008	0.131	0.408	0.596	-----	0.818	0.284	0.070	0.019	0.004	KURU	0.040
30	0.008	0.131	0.446	0.596	-----	0.757	0.284	0.070	0.019	0.004	KURU	0.040
31	0.029	-----	1.17	0.646	-----	0.696	-----	0.070	-----	0.004	KURU	-----
Maks.	0.208	0.304	5.33	1.72	16.7	8.27	0.646	0.284	0.332	0.019	0.004	0.040
Min.	0.008	0.052	0.112	0.179	0.696	0.696	0.284	0.070	0.019	0.004	KURU	KURU
Ortalama	0.017	0.189	0.351	0.458	3.41	2.19	0.435	0.188	0.071	0.010	0.000	0.004
LT/SN/Km2	0.272	2.96	5.48	7.16	53.3	34.2	6.80	2.94	1.11	0.152	0.008	0.062
AKIM mm.	0.729	7.67	14.7	19.2	129.	91.6	17.6	7.87	2.86	0.408	0.020	0.161
MİL. M3	0.047	0.491	0.940	1.23	8.26	5.86	1.13	0.504	0.183	0.026	0.001	0.010

SU YILI (2006) YILLIK TOPLAM AKIM 18.68 MİLYON M3 292 MM. 9.3 LT/SN/Km2

05. Gediz Havzasi

D05A044 DEMİRBÜKEN D. BASLAMIS

YERİ : **AKHİSAR SINDIRGI DEVLET KARAYOLUNUN 25.KM.SİNDEKİ KÖPRÜDEDİR. J19-C3**
27°57'58" Doğu - 39°3'46" Kuzey

YAĞIŞ ALANI : **148,00 km2** **YAKLAŞIK KOT : 205 m**

GÖZLEM SÜRESİ : **01.10.1990 - 30.09.2006**

ORTALAMA AKIMLAR : **Gözlem süresinde 0.597 m3/sn. (6 Yıllık) 2006 Su yılında 0.650 m3/sn.**

ANLIK EN ÇOK VE EN AZ AKIMLAR:

2006 Su yılında anlık ençok akım	**:**	**12.7**	**m3/sn**	**11.03.2006**
2006 Su yılında anlık enaz akım	**:**	**0.000**	**m3/sn**	**01.10.2005**
Gözlem süresinde anlık ençok akım	**:**	**18.7**	**m3/sn**	**25.12.2001**
Gözlem süresinde anlık enaz akım	**:**	**0.000**	**m3/sn**	**01.10.2000**

1. Anahtar Eğrisi (Seviyeler cm olarak)

Seviye	Akım	Seviye	Akım	Seviye	Akım	Seviye	Akım
1	0.000	16	0.046	41	1.9	141	13.3
4	0.000	19	0.098	61	4.1	151	14.6
7	0.000	22	0.210	91	7.4	161	15.9
10	0.003	25	0.370	121	10.8	171	17.3
13	0.015	30	0.750	131	12.0	202	0.000

Akımlar 01 Ekim 2005 'den 30 Eylül 2006' a kadar m3/sn olarak

Gün	Ekim	Kasım	Aralık	Ocak	Şubat	Mart	Nisan	Mayıs	Haziran	Temmuz	Ağustos	Eylül
01	KURU	0.057	0.200	0.690	1.21	3.66	1.05	0.480	0.053	KURU	KURU	KURU
02	KURU	0.033	0.200	0.620	1.21	3.77	0.955	0.480	0.053	KURU	KURU	KURU
03	0.007	0.057	0.176	0.550	1.21	4.76	0.955	0.480	0.037	KURU	KURU	KURU
04	0.081	0.057	0.152	0.480	1.21	4.76	0.955	0.480	0.037	KURU	KURU	KURU
05	0.057	0.057	0.152	0.480	1.36	4.43	0.860	0.385	0.037	KURU	KURU	KURU
06	0.033	0.057	0.176	0.480	2.58	4.21	0.860	0.385	0.037	KURU	KURU	KURU
07	0.033	0.081	0.176	0.410	5.24	3.99	0.860	0.480	0.037	KURU	KURU	KURU
08	0.009	0.081	0.176	0.410	4.76	4.10	0.860	0.480	0.037	KURU	KURU	KURU
09	0.004	0.081	0.550	0.410	4.52	3.66	0.860	0.385	0.053	KURU	KURU	KURU
10	KURU	0.081	0.480	0.410	6.32	3.22	0.765	0.385	0.069	KURU	KURU	KURU
11	KURU	0.081	0.410	0.340	5.48	5.09	0.765	0.290	0.053	KURU	KURU	KURU
12	KURU	0.081	0.410	0.340	3.32	6.41	0.670	0.290	0.053	KURU	KURU	KURU
13	0.033	0.081	0.410	0.340	2.40	0.195	0.670	0.290	0.053	KURU	KURU	KURU
14	0.007	0.105	0.340	0.340	2.30	0.575	0.670	0.290	0.053	KURU	KURU	KURU
15	0.007	0.105	0.410	0.340	1.92	0.385	0.765	0.290	0.053	KURU	KURU	KURU
16	0.007	0.105	0.410	0.340	1.78	0.195	0.670	0.290	0.053	KURU	KURU	KURU
17	0.009	0.128	0.620	0.340	1.92	0.195	0.575	0.195	0.053	KURU	KURU	KURU
18	0.009	0.480	0.760	0.340	1.92	1.34	0.575	0.195	0.037	KURU	KURU	KURU
19	0.007	0.340	3.83	5.61	2.20	1.92	0.670	0.100	0.037	KURU	KURU	KURU
20	0.007	0.620	0.900	2.04	2.06	1.92	0.670	0.100	0.028	KURU	KURU	KURU
21	0.007	0.340	0.690	0.775	2.06	1.63	0.575	0.100	0.028	KURU	KURU	KURU
22	0.007	0.270	0.690	0.340	2.06	1.49	0.575	0.100	0.018	KURU	KURU	KURU
23	0.007	0.200	0.550	2.40	2.06	1.49	0.575	0.084	0.018	KURU	KURU	KURU
24	0.007	0.176	0.480	2.22	2.06	1.49	0.575	0.084	0.015	KURU	KURU	KURU
25	0.007	0.340	0.340	1.68	3.56	1.34	0.575	0.084	0.012	KURU	KURU	0.008
26	0.009	1.88	0.340	1.50	4.32	1.05	0.480	0.084	0.010	KURU	KURU	0.037
27	0.009	1.55	0.340	1.36	3.88	0.955	0.480	0.069	0.007	KURU	KURU	0.037
28	0.009	0.620	0.270	1.36	3.66	0.860	0.480	0.069	KURU	KURU	KURU	0.007
29	0.009	0.480	0.340	1.21	-----	0.860	0.575	0.069	KURU	KURU	KURU	0.670
30	0.009	0.340	0.340	1.21	-----	0.860	0.575	0.069	KURU	KURU	KURU	0.037
31	0.033	-----	0.690	1.21	-----	1.20	-----	0.053	-----	KURU	KURU	-----
Maks.	0.270	3.18	5.28	7.26	9.79	12.7	1.05	0.480	0.069	KURU	KURU	1.92
Min.	KURU	0.033	0.152	0.050	1.21	0.195	0.480	0.053	KURU	KURU	KURU	KURU
Ortalama	0.014	0.299	0.516	0.986	2.81	2.32	0.705	0.246	0.034	KURU	KURU	0.027
LT/SN/Km2	0.092	2.02	3.49	6.66	19.0	15.7	4.76	1.66	0.232	0.000	0.000	0.179
AKIM mm.	0.247	5.23	9.35	17.8	45.9	42.0	12.3	4.45	0.602	0.000	0.000	0.465
MİL. M3	0.037	0.774	1.38	2.64	6.79	6.22	1.83	0.658	0.089	0.000	0.000	0.069

SU YILI (2006) YILLIK TOPLAM AKIM 20.49 MİLYON M3 138 MM. 4.4 LT/SN/Km2

05. Gediz Havzasi

D05A048 DEGİRMENDERE DOGANLAR

YERİ : **SALİHLİ YEŞİLKAVAK-DOĞANLAR YOLUNUN 15. KM SİNDEDİR.PAFTA L20A2**
28°14'40" Doğu - 38°25'44" Kuzey

YAĞIŞ ALANI : **41,80 km2** **YAKLAŞIK KOT : 200 m**

GÖZLEM SÜRESİ : **01.10.1998 - 30.09.2006**

ORTALAMA AKIMLAR : **Gözlem süresinde 0.535 m3/sn. (7 Yıllık) 2006 Su yılında 0.696 m3/sn.**

ANLIK EN ÇOK VE EN AZ AKIMLAR:

2006 Su yılında anlık ençok akım	:	**30.0**	**m3/sn**	**10.02.2006**
2006 Su yılında anlık enaz akım	:	**0.000**	**m3/sn**	**01.10.2005**
Gözlem süresinde anlık ençok akım	:	**30.0**	**m3/sn**	**10.02.2006**
Gözlem süresinde anlık enaz akım	:	**0.000**	**m3/sn**	**01.10.1999**

5. Anahtar Eğrisi (Seviyeler cm olarak)

Seviye	Akım	Seviye	Akım	Seviye	Akım	Seviye	Akım
1	0.000	12	0.025	30	0.312	130	16.1
3	0.002	14	0.035	40	0.794	150	21.9
6	0.006	16	0.047	50	1.6	155	23.4
8	0.010	18	0.064	76	4.8	170	28.9
10	0.016	20	0.086	100	9.3	180	32.6

Akımlar 01 Ekim 2005 'den 30 Eylül 2006' a kadar m3/sn olarak

Gün	Ekim	Kasım	Aralık	Ocak	Şubat	Mart	Nisan	Mayıs	Haziran	Temmuz	Ağustos	Eylül
01	KURU	KURU	0.794	2.12	1.48	0.853	0.500	0.350	0.134	KURU	KURU	KURU
02	KURU	KURU	0.676	1.48	1.79	0.853	0.425	0.350	0.134	KURU	KURU	KURU
03	KURU	KURU	0.676	1.30	1.68	0.971	0.425	0.387	0.118	KURU	KURU	KURU
04	KURU	KURU	0.559	1.03	1.57	0.912	0.425	0.387	0.118	KURU	KURU	KURU
05	KURU	KURU	0.500	1.39	6.79	0.912	0.425	0.425	0.102	KURU	KURU	KURU
06	KURU	KURU	0.500	1.90	15.6	0.794	0.387	0.425	0.102	KURU	KURU	KURU
07	KURU	KURU	0.500	2.01	13.2	0.853	0.387	0.462	0.118	KURU	KURU	KURU
08	KURU	KURU	0.425	1.79	9.92	0.971	0.387	0.425	0.118	KURU	KURU	KURU
09	KURU	KURU	0.312	1.30	8.14	1.12	0.387	0.425	0.118	KURU	KURU	KURU
10	KURU	KURU	0.312	1.03	6.40	1.39	0.387	0.350	0.102	KURU	KURU	KURU
11	KURU	KURU	0.312	0.912	4.39	2.12	0.312	0.350	0.102	KURU	KURU	KURU
12	KURU	KURU	0.312	0.794	3.96	4.68	0.312	0.387	0.118	KURU	KURU	KURU
13	KURU	0.016	0.283	0.735	3.52	3.67	0.312	0.350	0.118	KURU	KURU	KURU
14	KURU	0.029	0.166	0.618	3.23	2.46	0.350	0.387	0.102	KURU	KURU	KURU
15	KURU	0.040	0.102	0.559	3.01	2.34	0.350	0.387	0.102	KURU	KURU	KURU
16	KURU	0.064	0.102	0.500	2.68	2.23	0.350	0.350	0.102	KURU	KURU	KURU
17	KURU	0.387	0.056	0.462	2.46	2.12	0.312	0.312	0.073	KURU	KURU	KURU
18	KURU	1.57	0.040	0.425	2.01	1.79	0.312	0.254	0.073	KURU	KURU	KURU
19	KURU	0.500	0.020	2.12	1.90	1.57	0.350	0.254	0.064	KURU	KURU	KURU
20	KURU	0.254	0.016	2.79	1.39	1.39	0.387	0.254	0.047	KURU	KURU	KURU
21	KURU	0.283	0.016	1.57	1.21	1.12	0.350	0.195	0.035	KURU	KURU	KURU
22	KURU	0.387	0.254	1.21	1.21	1.12	0.350	0.195	0.025	KURU	KURU	KURU
23	KURU	0.676	0.853	1.39	1.12	1.12	0.387	0.166	0.016	KURU	KURU	KURU
24	KURU	1.39	0.735	1.30	1.12	0.971	0.350	0.166	KURU	KURU	KURU	KURU
25	KURU	4.83	0.618	1.21	1.03	0.971	0.350	0.195	KURU	KURU	KURU	KURU
26	KURU	7.95	0.559	0.971	1.03	0.971	0.312	0.150	KURU	KURU	KURU	KURU
27	KURU	4.68	0.500	1.30	0.971	0.794	0.283	0.150	KURU	KURU	KURU	KURU
28	KURU	2.68	0.500	1.79	0.971	0.794	0.254	0.134	KURU	KURU	KURU	KURU
29	KURU	1.68	1.30	1.68	-----	0.676	0.312	0.134	KURU	KURU	KURU	KURU
30	KURU	1.12	0.971	1.57	-----	0.618	0.387	0.118	KURU	KURU	KURU	KURU
31	KURU	-----	2.46	1.57	-----	0.500	-----	0.118	-----	KURU	KURU	-----
Maks.	KURU	10.3	3.23	6.79	30.0	6.59	0.618	0.462	0.134	KURU	KURU	KURU
Min.	KURU	KURU	0.016	0.425	0.971	0.500	0.254	0.086	KURU	KURU	KURU	KURU
Ortalama	KURU	0.951	0.498	1.32	3.71	1.41	0.361	0.290	0.071	KURU	KURU	KURU
LT/SN/Km2	0.000	22.8	11.9	31.5	88.7	33.7	8.63	6.94	1.71	0.000	0.000	0.000
AKIM mm.	0.000	59.0	31.9	84.4	215.	90.2	22.4	18.6	4.43	0.000	0.000	0.000
MİL. M3	0.000	2.47	1.33	3.53	8.97	3.77	0.935	0.777	0.185	0.000	0.000	0.000

SU YILI (2006) YILLIK TOPLAM AKIM 21.97 MİLYON M3 526 MM. 16.7 LT/SN/Km2

05. Gediz Havzasi

D05A049 KAYACIK D. ÇAGLAYAN

YERİ : **AKHİSAR İLÇESİ ÇAĞLAYAN KÖYÜNDEKİ STABLİZE YOLUN 2.5 KM SİNDEDİR.PAFTA K20A4 28°3'12" Doğu - 38°48'25" Kuzey**

YAĞIŞ ALANI : **299,30 km2** **YAKLAŞIK KOT : 220 m**

GÖZLEM SÜRESİ : **01.10.1993 - 30.09.2006**

ORTALAMA AKIMLAR : **Gözlem süresinde 1.082 m3/sn. (3 Yıllık) 2006 Su yılında 1.416 m3/sn.**

ANLIK EN ÇOK VE EN AZ AKIMLAR:

2006 Su yılında anlık ençok akım	**:**	**58.4**	**m3/sn**	**12.03.2006**
2006 Su yılında anlık enaz akım	**:**	**0.011**	**m3/sn**	**01.10.2005**
Gözlem süresinde anlık ençok akım	**:**	**58.4**	**m3/sn**	**12.03.2006**
Gözlem süresinde anlık enaz akım	**:**	**0.004**	**m3/sn**	**23.08.2005**

3. Anahtar Eğrisi (Seviyeler cm olarak)

Akımlar 01 Ekim 2005 'den 30 Eylül 2006' a kadar m3/sn olarak

Gün	Ekim	Kasım	Aralık	Ocak	Şubat	Mart	Nisan	Mayıs	Haziran	Temmuz	Ağustos	Eylül
01	0.011	0.023	0.458	1.95	1.48	3.62	2.42	1.64	0.406	0.253	0.353	0.093
02	0.023	0.033	0.458	1.95	1.48	3.22	2.42	1.64	0.353	0.203	0.353	0.093
03	0.033	0.033	0.458	1.95	1.64	7.64	2.42	1.64	0.353	0.203	0.353	0.069
04	0.023	0.033	0.458	2.11	1.48	5.63	4.43	1.48	0.353	0.203	0.353	0.020
05	0.023	0.033	0.458	2.11	1.17	4.43	3.22	1.48	0.353	0.203	0.353	0.020
06	0.023	0.033	0.458	2.11	1.17	4.03	2.42	1.48	0.353	0.203	0.353	0.044
07	0.013	0.033	0.406	3.62	1.17	5.63	2.42	1.32	0.353	0.203	0.353	0.069
08	0.013	0.033	0.406	3.62	0.854	8.04	2.26	1.32	0.353	0.203	0.353	0.069
09	0.013	0.033	0.406	3.62	0.854	6.03	2.11	1.32	0.406	0.160	0.353	0.093
10	0.011	0.033	0.353	3.22	0.854	5.23	2.11	1.17	0.458	0.203	0.353	0.093
11	0.013	0.033	0.353	3.22	0.709	8.44	2.11	1.17	0.406	0.203	0.353	0.093
12	0.013	0.033	0.353	2.42	0.709	21.3	1.95	1.17	0.406	0.203	0.353	0.069
13	0.043	0.033	0.303	2.26	0.709	6.84	1.95	1.01	0.353	0.203	0.303	0.117
14	0.023	0.033	0.303	2.26	0.563	9.24	1.95	1.01	0.353	0.160	0.253	0.117
15	0.023	0.033	0.303	2.11	0.709	6.43	1.95	1.01	0.353	0.160	0.253	0.117
16	0.023	0.033	0.253	1.79	3.62	6.43	1.79	0.854	0.303	0.117	0.203	0.117
17	0.023	0.043	0.709	1.79	0.563	6.03	1.79	0.854	0.253	0.117	0.203	0.117
18	0.023	0.640	0.709	1.95	1.01	6.03	1.79	0.854	0.303	0.117	0.203	0.160
19	0.023	1.32	3.62	1.95	1.01	5.63	1.64	0.709	0.303	0.117	0.160	0.160
20	0.023	2.11	1.01	1.95	1.01	5.23	1.64	0.709	0.303	0.093	0.160	0.160
21	0.023	1.32	0.709	1.79	2.42	4.83	1.64	0.709	0.253	0.093	0.160	0.069
22	0.023	0.854	0.563	1.79	2.42	4.43	1.64	0.709	0.253	0.093	0.093	0.069
23	0.023	0.563	0.854	1.79	2.26	4.43	1.64	0.709	0.253	0.093	0.093	0.044
24	0.023	0.563	0.854	2.11	2.26	4.43	1.64	0.563	0.253	0.093	0.093	1.01
25	0.023	1.95	0.854	2.11	4.83	4.43	1.64	0.458	0.203	0.093	0.093	4.83
26	0.023	7.64	0.854	7.24	6.43	4.03	1.64	0.458	0.203	0.093	0.093	3.62
27	0.023	5.23	1.64	5.23	4.83	3.62	1.64	0.458	0.203	0.093	0.069	3.22
28	0.023	0.563	1.64	4.83	4.03	3.62	1.64	0.458	0.253	0.093	0.069	5.63
29	0.023	0.511	1.64	4.03	-----	3.22	1.64	0.458	0.253	0.093	0.093	12.3
30	0.023	0.511	1.64	2.26	-----	2.82	1.64	0.406	0.253	0.203	0.093	8.40
31	0.023	-----	1.79	2.26	-----	2.82	-----	0.406	-----	0.353	0.093	-----
Maks.	0.053	22.9	19.7	8.44	9.65	58.4	15.7	1.64	0.458	0.353	0.353	18.5
Min.	0.011	0.023	0.253	1.79	0.563	2.82	1.64	0.406	0.203	0.093	0.069	0.020
Ortalama	0.022	0.811	0.815	2.69	1.87	5.73	2.04	0.956	0.315	0.159	0.226	1.37
LT/SN/Km2	0.072	2.71	2.72	8.99	6.23	19.2	6.81	3.19	1.05	0.530	0.756	4.58
AKIM mm.	0.193	7.03	7.30	24.1	15.1	51.3	17.7	8.55	2.73	1.42	2.03	11.9
MİL. M3	0.058	2.10	2.18	7.21	4.51	15.4	5.29	2.56	0.817	0.425	0.606	3.55

SU YILI (2006) YILLIK TOPLAM AKIM 44.71 MİLYON M3 149 MM. 4.7 LT/SN/Km2

05. Gediz Havzasi

D05A050 AYAN D. ÇAMURKÖY

YERİ : **KULA SELENDİ YOLUNUN ÇAMURKÖYDEN 1KM.SONRA KARAYOLU KÖPRÜSÜNDEDİR.PAFTA K22-A4**
29°1'0" Doğu - 38°45'0" Kuzey

YAĞIŞ ALANI : **59,50 km2** **YAKLAŞIK KOT : 740 m**

GÖZLEM SÜRESİ : **01.10.1998 - 30.09.2006**

ORTALAMA AKIMLAR : **Gözlem süresinde 0.336 m3/sn. (6 Yıllık) 2006 Su yılında 0.413 m3/sn.**

ANLIK EN ÇOK VE EN AZ AKIMLAR:

2006 Su yılında anlık ençok akım	**:**	**29.0**	**m3/sn**	**19.01.2006**
2006 Su yılında anlık enaz akım	**:**	**0.000**	**m3/sn**	**01.10.2005**
Gözlem süresinde anlık ençok akım	**:**	**87.8**	**m3/sn**	**17.12.2001**
Gözlem süresinde anlık enaz akım	**:**	**0.000**	**m3/sn**	**15.06.2001**

4. Anahtar Eğrisi (Seviyeler cm olarak)

Seviye	Akım	Seviye	Akım	Seviye	Akım	Seviye	Akım
5	0.003	30	6.7	60	17.4	110	42.0
7	0.049	35	8.4	70	21.2	120	47.2
10	0.549	40	10.4	80	26.4	130	52.4
20	3.2	50	13.6	90	31.6	140	57.6
25	4.9	55	15.5	100	36.8	200	90.0

Akımlar 01 Ekim 2005 'den 30 Eylül 2006' a kadar m3/sn olarak

Gün	Ekim	Kasım	Aralık	Ocak	Şubat	Mart	Nisan	Mayıs	Haziran	Temmuz	Ağustos	Eylül
01	KURU	KURU	0.045	1.07	0.549	0.549	0.217	0.010	KURU	KURU	KURU	KURU
02	KURU	KURU	0.045	0.549	0.807	0.549	0.217	0.045	KURU	KURU	KURU	KURU
03	KURU	KURU	0.045	0.549	0.549	0.807	0.217	0.045	KURU	KURU	KURU	KURU
04	KURU	KURU	0.045	0.549	0.807	0.549	0.217	0.045	KURU	KURU	KURU	KURU
05	KURU	KURU	0.045	0.549	0.807	0.349	0.217	0.428	KURU	KURU	KURU	KURU
06	KURU	KURU	0.045	0.549	2.90	0.349	0.217	0.110	KURU	KURU	KURU	KURU
07	KURU	KURU	0.045	0.549	2.33	0.349	0.110	0.110	KURU	KURU	KURU	KURU
08	KURU	KURU	0.045	0.549	1.03	4.86	0.110	0.217	KURU	KURU	KURU	KURU
09	KURU	KURU	0.045	0.349	1.03	2.90	0.110	0.110	KURU	KURU	KURU	KURU
10	KURU	KURU	0.045	0.349	2.02	1.24	0.110	0.110	KURU	KURU	KURU	KURU
11	KURU	KURU	0.045	0.199	15.6	1.24	0.110	0.110	KURU	KURU	KURU	KURU
12	KURU	KURU	0.045	0.199	7.41	1.24	0.110	0.110	KURU	KURU	KURU	KURU
13	KURU	KURU	0.045	0.199	3.53	1.24	0.110	0.045	KURU	KURU	KURU	KURU
14	KURU	KURU	0.045	0.199	3.20	6.44	0.110	0.045	KURU	KURU	KURU	KURU
15	KURU	KURU	0.045	0.199	2.93	3.12	0.110	0.010	KURU	KURU	KURU	KURU
16	KURU	KURU	0.045	0.049	2.93	1.11	0.110	0.045	KURU	KURU	KURU	KURU
17	KURU	KURU	0.110	0.049	2.93	0.910	0.110	0.045	KURU	KURU	KURU	KURU
18	KURU	0.428	0.045	0.049	2.93	0.910	0.110	0.010	KURU	KURU	KURU	KURU
19	KURU	0.630	1.24	2.93	2.93	0.428	0.045	0.010	KURU	KURU	KURU	KURU
20	KURU	1.49	0.217	4.54	2.38	0.254	0.010	0.010	KURU	KURU	KURU	KURU
21	KURU	0.630	0.045	2.38	0.807	1.03	KURU	KURU	KURU	KURU	KURU	KURU
22	KURU	0.428	0.045	1.58	0.349	0.630	0.010	KURU	KURU	KURU	KURU	KURU
23	KURU	0.110	0.045	1.07	0.349	0.630	0.110	KURU	KURU	KURU	KURU	KURU
24	KURU	0.045	0.010	0.807	0.349	0.630	0.045	KURU	KURU	KURU	KURU	KURU
25	KURU	0.428	0.010	0.807	0.349	0.630	0.010	KURU	KURU	KURU	KURU	KURU
26	KURU	5.84	0.010	0.807	0.549	0.630	0.010	KURU	KURU	KURU	KURU	KURU
27	KURU	3.44	0.010	0.807	0.807	0.630	0.010	KURU	KURU	KURU	KURU	KURU
28	KURU	2.02	0.010	0.807	0.549	0.630	0.045	KURU	KURU	KURU	KURU	KURU
29	KURU	1.03	0.217	0.807	-----	0.428	0.045	KURU	KURU	KURU	KURU	KURU
30	KURU	0.428	0.110	0.807	-----	0.428	0.010	KURU	KURU	KURU	KURU	KURU
31	KURU	-----	1.03	0.549	-----	0.428	-----	KURU	-----	KURU	KURU	-----
Maks.	KURU	14.0	3.98	29.0	24.8	15.6	0.630	0.813	KURU	KURU	KURU	KURU
Min.	KURU	KURU	0.010	0.049	0.349	0.254	KURU	KURU	KURU	KURU	KURU	KURU
Ortalama	KURU	0.565	0.125	0.821	2.28	1.17	0.099	0.054	KURU	KURU	KURU	KURU
LT/SN/Km2	0.000	9.49	2.10	13.8	38.2	19.6	1.66	0.905	0.000	0.000	0.000	0.000
AKIM mm.	0.000	24.6	5.63	37.0	92.5	52.4	4.32	2.43	0.000	0.000	0.000	0.000
MİL. M3	0.000	1.46	0.335	2.20	5.50	3.12	0.257	0.144	0.000	0.000	0.000	0.000

SU YILI (2006) YILLIK TOPLAM AKIM 13.02 MİLYON M3 219 MM. 6.9 LT/SN/Km2

05. Gediz Havzasi

D05A052 KARANOHUT D. KARANOHUT.

YERİ : **SALİHLI YENİPAZAR KARANOHUT YOLUNUN 13.KM SİNDEDIR.PAFTA L20A2**
28°12'27" Doğu - 38°25'19" Kuzey

YAĞIŞ ALANI : **15,50 km2** **YAKLAŞIK KOT : 587 m**

GÖZLEM SÜRESİ : **01.10.1998 - 30.09.2006**

ORTALAMA AKIMLAR : **Gözlem süresinde 0.276 m3/sn. (6 Yıllık) 2006 Su yılında 0.477 m3/sn.**

ANLIK EN ÇOK VE EN AZ AKIMLAR:

2006 Su yılında anlık ençok akım	:	**4.42**	**m3/sn**	**10.02.2006**
2006 Su yılında anlık enaz akım	:	**0.000**	**m3/sn**	**01.10.2005**
Gözlem süresinde anlık ençok akım	:	**14.9**	**m3/sn**	**25.12.2001**
Gözlem süresinde anlık enaz akım	:	**0.000**	**m3/sn**	**01.10.2000**

3. Anahtar Eğrisi (Seviyeler cm olarak)

Seviye	Akım	Seviye	Akım	Seviye	Akım	Seviye	Akım
1	0.000	16	0.000	46	0.428	121	9.2
4	0.000	19	0.000	81	2.8	131	10.9
7	0.000	22	0.000	91	4.3	141	12.6
10	0.000	25	0.000	101	5.8	151	14.5
13	0.000	32	0.016	111	7.5	156	15.4

Akımlar 01 Ekim 2005 'den 30 Eylül 2006' a kadar m3/sn olarak

Gün	Ekim	Kasım	Aralık	Ocak	Şubat	Mart	Nisan	Mayıs	Haziran	Temmuz	Ağustos	Eylül
01	KURU	KURU	0.317	1.25	1.41	1.57	1.33	0.289	0.204	KURU	KURU	KURU
02	KURU	KURU	0.289	1.09	1.49	1.49	1.33	0.289	0.204	KURU	KURU	KURU
03	KURU	KURU	0.261	0.931	1.49	1.57	1.33	0.261	0.204	KURU	KURU	KURU
04	KURU	KURU	0.232	0.852	1.49	1.57	1.33	0.261	0.204	KURU	KURU	KURU
05	KURU	KURU	0.204	1.01	1.49	1.41	1.25	0.261	0.204	KURU	KURU	KURU
06	KURU	KURU	0.176	1.25	2.84	1.33	1.25	0.261	0.204	KURU	KURU	KURU
07	KURU	KURU	0.176	1.25	2.55	1.49	1.25	0.261	0.204	KURU	KURU	KURU
08	KURU	KURU	0.148	1.25	2.17	1.90	1.25	0.261	0.204	KURU	KURU	KURU
09	KURU	KURU	0.176	0.852	1.90	1.65	1.25	0.261	0.204	KURU	KURU	KURU
10	KURU	KURU	0.119	0.695	2.74	1.41	1.25	0.261	0.204	KURU	KURU	KURU
11	KURU	KURU	0.119	0.616	3.99	1.49	1.17	0.261	0.204	KURU	KURU	KURU
12	KURU	0.002	0.119	0.616	3.26	2.74	0.616	0.261	0.204	KURU	KURU	KURU
13	KURU	0.006	0.119	0.567	2.08	2.26	0.663	0.261	0.204	KURU	KURU	KURU
14	KURU	0.009	0.091	0.518	1.25	2.08	0.663	0.232	0.176	KURU	KURU	KURU
15	KURU	0.011	0.176	0.518	1.09	1.73	0.569	0.232	0.035	KURU	KURU	KURU
16	KURU	0.016	0.119	0.470	0.931	1.49	0.522	0.232	0.006	KURU	KURU	KURU
17	KURU	0.091	0.148	0.470	0.931	1.33	0.522	0.232	0.006	KURU	KURU	KURU
18	KURU	0.317	0.569	0.421	1.01	1.17	0.475	0.232	0.002	KURU	KURU	KURU
19	KURU	0.232	1.26	1.09	1.17	0.931	0.475	0.232	KURU	KURU	KURU	KURU
20	KURU	0.176	1.41	1.41	1.17	0.774	0.475	0.232	KURU	KURU	KURU	KURU
21	KURU	0.148	1.01	1.01	1.17	0.774	0.428	0.232	KURU	KURU	KURU	KURU
22	KURU	0.119	0.852	0.852	1.09	0.774	0.428	0.232	KURU	KURU	KURU	KURU
23	KURU	0.261	0.774	0.931	1.09	1.01	0.428	0.232	KURU	KURU	KURU	KURU
24	KURU	0.475	0.616	0.852	1.01	1.33	0.373	0.232	KURU	KURU	KURU	KURU
25	KURU	1.01	0.567	0.774	1.49	1.41	0.373	0.204	KURU	KURU	KURU	KURU
26	KURU	1.72	0.518	0.695	1.73	1.41	0.317	0.204	KURU	KURU	KURU	KURU
27	KURU	1.13	0.518	0.695	1.57	1.25	0.289	0.204	KURU	KURU	KURU	KURU
28	KURU	0.804	0.518	0.567	1.49	1.17	0.289	0.204	KURU	KURU	KURU	KURU
29	KURU	0.569	1.01	1.01	-----	1.17	0.289	0.204	KURU	KURU	KURU	KURU
30	KURU	0.475	0.931	1.57	-----	1.41	0.261	0.204	KURU	KURU	KURU	KURU
31	KURU	-----	1.25	1.49	-----	1.41	-----	0.204	-----	KURU	KURU	-----
Maks.	KURU	2.06	1.98	2.17	4.42	3.05	1.33	0.428	0.317	KURU	KURU	KURU
Min.	KURU	KURU	0.091	0.421	0.931	0.774	0.261	0.204	KURU	KURU	KURU	KURU
Ortalama	KURU	0.252	0.477	0.889	1.68	1.44	0.748	0.240	0.096	KURU	KURU	KURU
LT/SN/Km2	0.000	16.3	30.8	57.4	109.	92.6	48.3	15.5	6.19	0.000	0.000	0.000
AKIM mm.	0.000	42.2	82.5	154.	262.	248.	125.	41.4	16.0	0.000	0.000	0.000
MİL. M3	0.000	0.654	1.28	2.38	4.07	3.85	1.94	0.642	0.249	0.000	0.000	0.000

SU YILI (2006) YILLIK TOPLAM AKIM 15.06 MİLYON M3 972 MM. 30.8 LT/SN/Km2

05. Gediz Havzasi

D05A053 ZEYTİNÇAY OSMANİYE

YERİ : **ALAŞEHİR OSMANİYE KÖYYOLUNUN YAKLAŞIK 4KM SİNDEKİ KÖPRÜNÜN MEMBASINDA BENDİN ÜZERİNDEDİR**
PAFTA L20B3
28°28'41" Doğu - 38°21'2" Kuzey

YAĞIŞ ALANI : **31,70 km2** **YAKLAŞIK KOT : 273 m**

GÖZLEM SÜRESİ : **05.01.2001 - 30.09.2006**

ORTALAMA AKIMLAR : **Gözlem süresinde 0.360 m3/sn. (4 Yıllık) 2006 Su yılında 0.453 m3/sn.**

ANLIK EN ÇOK VE EN AZ AKIMLAR:

2006 Su yılında anlık ençok akım	**:**	**34.0**	**m3/sn**	**11.02.2006**
2006 Su yılında anlık enaz akım	**:**	**0.000**	**m3/sn**	**01.10.2005**
Gözlem süresinde anlık ençok akım	**:**	**34.0**	**m3/sn**	**11.02.2006**
Gözlem süresinde anlık enaz akım	**:**	**0.000**	**m3/sn**	**17.08.2003**

4. Anahtar Eğrisi (Seviyeler cm olarak)

Seviye	Akım	Seviye	Akım	Seviye	Akım	Seviye	Akım
1	0.000	40	3.1	170	26.8	260	43.9
4	0.001	60	6.2	200	32.5	270	45.8
7	0.025	80	9.8	230	38.2	280	47.7
10	0.110	110	15.4	240	40.1	290	49.6
25	1.2	140	21.1	250	42.0	300	51.5

Akımlar 01 Ekim 2005 'den 30 Eylül 2006' a kadar m3/sn olarak

Gün	Ekim	Kasım	Aralık	Ocak	Şubat	Mart	Nisan	Mayıs	Haziran	Temmuz	Ağustos	Eylül
01	KURU	KURU	0.364	0.504	0.364	1.32	1.01	0.176	0.034	0.034	KURU	KURU
02	KURU	KURU	0.230	0.435	0.364	1.32	1.01	0.176	0.034	0.034	KURU	KURU
03	KURU	KURU	0.061	0.364	0.292	1.32	0.913	0.176	0.034	0.094	KURU	KURU
04	KURU	KURU	0.061	0.364	0.292	1.42	1.11	0.176	0.034	0.132	KURU	KURU
05	KURU	KURU	0.061	0.435	0.292	1.42	1.11	0.176	0.034	0.132	KURU	KURU
06	KURU	KURU	0.061	0.504	1.15	1.42	0.648	0.176	0.034	0.132	KURU	KURU
07	KURU	KURU	0.061	0.572	0.805	1.52	0.648	0.176	0.034	0.094	KURU	KURU
08	KURU	KURU	0.061	0.504	0.648	1.52	0.648	0.176	0.034	0.061	KURU	KURU
09	KURU	0.006	0.061	0.435	0.572	1.52	0.648	0.176	0.034	0.061	KURU	KURU
10	KURU	0.006	0.061	0.364	1.25	1.52	0.572	0.176	0.034	0.061	KURU	KURU
11	KURU	0.006	0.061	0.364	29.0	1.42	0.504	0.176	0.034	0.094	KURU	KURU
12	KURU	0.006	0.061	0.292	13.6	1.42	0.504	0.176	0.034	0.094	KURU	KURU
13	KURU	0.018	0.061	0.292	6.71	1.52	0.504	0.176	0.034	0.094	KURU	KURU
14	KURU	0.018	0.132	0.230	4.28	1.42	0.504	0.132	0.034	0.061	KURU	KURU
15	KURU	0.018	0.132	0.230	2.17	1.52	0.435	0.132	0.018	0.061	KURU	KURU
16	KURU	0.061	0.094	0.176	1.78	1.32	0.435	0.176	0.018	0.061	KURU	KURU
17	KURU	0.061	0.094	0.176	1.78	1.21	0.292	0.176	0.018	0.061	KURU	KURU
18	KURU	0.061	0.094	0.176	1.65	1.11	0.292	0.176	0.018	0.061	KURU	KURU
19	KURU	0.061	0.648	0.887	1.65	1.01	0.292	0.176	0.018	0.061	KURU	KURU
20	KURU	0.094	0.230	1.15	1.52	0.913	0.292	0.132	0.018	0.018	KURU	KURU
21	KURU	0.094	0.132	0.723	1.65	0.913	0.230	0.094	0.018	0.006	KURU	KURU
22	KURU	0.132	0.094	0.572	1.52	0.913	0.230	0.094	0.018	KURU	KURU	KURU
23	KURU	0.132	0.094	0.648	1.52	1.11	0.230	0.061	0.018	KURU	KURU	KURU
24	KURU	0.176	0.132	0.572	1.42	1.42	0.176	0.061	0.006	KURU	KURU	KURU
25	KURU	0.364	0.061	0.504	1.42	1.32	0.176	0.061	0.006	KURU	KURU	KURU
26	KURU	1.88	0.094	0.435	1.42	1.32	0.176	0.061	0.018	KURU	KURU	KURU
27	KURU	0.805	0.094	0.364	1.32	1.11	0.176	0.061	0.132	KURU	KURU	KURU
28	KURU	0.572	0.061	0.364	1.32	1.01	0.176	0.061	0.094	KURU	KURU	KURU
29	KURU	0.435	0.176	0.364	-----	1.01	0.176	0.061	0.094	KURU	KURU	KURU
30	KURU	0.435	0.176	0.364	-----	1.11	0.176	0.061	0.061	KURU	KURU	KURU
31	KURU	-----	0.364	0.292	-----	1.11	-----	0.061	-----	KURU	KURU	-----
Maks.	KURU	4.37	2.11	3.46	34.0	1.91	2.44	0.435	2.11	2.23	KURU	KURU
Min.	KURU	KURU	0.018	0.176	0.292	0.816	0.176	0.061	0.006	KURU	KURU	KURU
Ortalama	KURU	0.181	0.134	0.441	2.92	1.27	0.476	0.133	0.035	0.049	KURU	KURU
LT/SN/Km2	0.000	5.72	4.24	13.9	92.1	40.2	15.0	4.20	1.10	1.53	0.000	0.000
AKIM mm.	0.000	14.8	11.4	37.2	223.	108.	39.0	11.2	2.86	4.11	0.000	0.000
MİL. M3	0.000	0.470	0.360	1.18	7.06	3.41	1.23	0.356	0.091	0.130	0.000	0.000

SU YILI (2006) YILLIK TOPLAM AKIM 14.29 MİLYON M3 451 MM. 14.3 LT/SN/Km2

05. Gediz Havzasi

D05A055 GÜRLEVİK D. AKÇAPINAR

YERİ : **TURGUTLU AKCAPINAR KASABASINDAN 2.5KM.SONRA ISTASYONA VARILIR.PAFTA L19-B1**
27°50'52" Doğu - 38°27'26" Kuzey

YAĞIŞ ALANI : **43,13 km2** **YAKLAŞIK KOT : 155 m**

GÖZLEM SÜRESİ : **19.03.2002 - 30.09.2006**

ORTALAMA AKIMLAR : **Gözlem süresinde 0.435 m3/sn. (4 Yıllık) 2006 Su yılında 0.509 m3/sn.**

ANLIK EN ÇOK VE EN AZ AKIMLAR:

2006 Su yılında anlık ençok akım	**:**	**18.4**	**m3/sn**	**11.02.2006**
2006 Su yılında anlık enaz akım	**:**	**0.000**	**m3/sn**	**05.07.2006**
Gözlem süresinde anlık ençok akım	**:**	**36.0**	**m3/sn**	**30.01.2004**
Gözlem süresinde anlık enaz akım	**:**	**0.000**	**m3/sn**	**11.02.2003**

2. Anahtar Eğrisi (Seviyeler cm olarak)

Seviye	Akım	Seviye	Akım	Seviye	Akım	Seviye	Akım
16	0.000	30	0.373	80	10.4	130	26.4
20	0.018	34	0.824	90	13.6	140	29.6
22	0.050	40	1.5	100	16.8	150	32.8
24	0.082	49	2.7	110	20.0	160	36.0
26	0.148	60	4.8	120	23.2	165	37.6

Akımlar 01 Ekim 2005 'den 30 Eylül 2006' a kadar m3/sn olarak

Gün	Ekim	Kasım	Aralık	Ocak	Şubat	Mart	Nisan	Mayıs	Haziran	Temmuz	Ağustos	Eylül
01	0.013	0.010	0.104	0.314	0.824	1.24	1.24	0.148	0.050	0.050	0.018	0.018
02	0.013	0.010	0.104	0.255	0.824	1.24	1.13	0.148	0.050	0.050	0.018	0.018
03	0.013	0.010	0.104	0.202	0.824	1.13	1.13	0.148	0.050	0.050	0.018	0.018
04	0.010	0.010	0.082	0.148	0.824	1.13	1.03	0.148	0.050	0.050	0.018	0.018
05	0.010	0.010	0.082	0.148	0.824	1.13	1.03	0.148	0.050	0.040	0.018	0.018
06	0.010	0.010	0.082	0.202	3.41	1.13	1.03	0.148	0.050	0.018	0.018	0.018
07	0.010	0.010	0.066	0.314	1.99	1.86	0.926	0.148	0.050	0.018	0.018	0.018
08	0.010	0.010	0.082	0.475	1.47	3.61	0.926	0.148	0.050	0.018	0.018	0.018
09	0.010	0.010	0.314	0.373	1.36	1.73	0.824	0.255	0.050	0.018	0.018	0.018
10	0.010	0.010	0.104	0.314	5.77	1.36	0.824	0.104	0.050	0.018	0.018	0.018
11	0.010	0.010	0.082	0.255	9.14	1.86	0.824	0.066	0.050	0.018	0.018	0.018
12	0.010	0.010	0.066	0.202	3.07	3.41	0.701	0.066	0.050	0.018	0.018	0.018
13	0.010	0.010	0.066	0.148	1.73	3.41	0.701	0.066	0.202	0.018	0.018	0.018
14	0.010	0.010	0.066	0.148	1.24	2.43	0.577	0.066	0.066	0.018	0.018	0.018
15	0.010	0.010	0.314	0.148	1.03	1.60	0.577	0.066	0.050	0.018	0.018	0.018
16	0.010	0.010	0.082	0.148	1.03	1.13	0.577	0.066	0.050	0.018	0.018	0.018
17	0.010	0.018	0.050	0.148	1.03	1.03	0.475	0.066	0.050	0.018	0.018	0.018
18	0.010	1.86	1.60	0.104	1.03	1.13	0.475	0.040	0.050	0.018	0.018	0.018
19	0.013	1.60	2.89	1.86	1.03	1.03	0.373	0.040	0.050	0.018	0.018	0.018
20	0.010	2.28	1.60	2.28	1.03	1.03	0.373	0.040	0.050	0.018	0.018	0.018
21	0.010	2.28	1.24	0.926	1.03	1.03	0.373	0.040	0.050	0.018	0.018	0.018
22	0.010	2.14	0.926	0.824	1.03	1.03	0.314	0.040	0.050	0.018	0.018	0.018
23	0.010	2.14	0.577	1.03	1.03	1.03	0.314	0.040	0.050	0.018	0.018	0.018
24	0.010	2.14	0.255	0.824	1.03	1.13	0.255	0.040	0.050	0.018	0.018	0.040
25	0.010	3.61	0.202	0.824	1.03	1.24	0.255	0.040	0.050	0.018	0.018	0.018
26	0.010	5.04	0.148	0.824	1.24	1.24	0.255	0.040	0.050	0.018	0.018	0.013
27	0.010	5.04	0.082	0.824	1.24	1.24	0.202	0.040	0.050	0.018	0.018	0.010
28	0.010	5.04	0.082	0.824	1.24	1.24	0.202	0.029	0.050	0.018	0.018	0.024
29	0.010	1.60	0.104	0.824	-----	1.24	0.148	0.040	0.050	0.018	0.018	1.03
30	0.010	0.104	0.104	0.824	-----	1.24	0.148	0.050	0.050	0.018	0.018	0.926
31	0.010	-----	0.255	0.824	-----	1.24	-----	0.050	-----	0.018	0.018	-----
Maks.	0.013	5.04	15.8	15.2	18.4	14.9	1.36	1.86	7.00	0.475	0.018	11.7
Min.	0.010	0.010	0.050	0.104	0.824	1.03	0.148	0.029	0.050	KURU	0.018	0.010
Ortalama	0.010	1.17	0.384	0.566	1.73	1.50	0.607	0.083	0.056	0.023	0.018	0.083
LT/SN/Km2	0.241	27.1	8.91	13.1	40.0	34.8	14.1	1.93	1.29	0.530	0.417	1.91
AKIM mm.	0.645	70.2	23.9	35.2	96.9	93.2	36.5	5.16	3.34	1.42	1.12	4.96
MİL. M3	0.028	3.03	1.03	1.52	4.18	4.02	1.57	0.222	0.144	0.061	0.048	0.214

SU YILI (2006) YILLIK TOPLAM AKIM 16.07 MİLYON M3 373 MM. 11.8 LT/SN/Km2

05. Gediz Havzasi

D05A056 KAVAKLIDERE DEREKÖY

YERİ : **SALIHLI ALAŞEHİR YOLUNUN 21.KM.SİNDEN SAĞA DÖNÜLEREK KAVAKLIDERE KÖYÜNE VARILIR KÖYDEN 10 KM. SONRA ISTASYONA VARILIR. L20 B1**
28°19'28" Doğu - 38°22'44" Kuzey

YAĞIŞ ALANI : **98,65 km2** **YAKLAŞIK KOT : 260 m**

GÖZLEM SÜRESİ : **02.04.2002 - 30.09.2006**

ORTALAMA AKIMLAR : **Gözlem süresinde 1.312 m3/sn. (4 Yıllık) 2006 Su yılında 1.804 m3/sn.**

ANLIK EN ÇOK VE EN AZ AKIMLAR:

2006 Su yılında anlık ençok akım	**:**	**38.3**	**m3/sn**	**11.02.2006**
2006 Su yılında anlık enaz akım	**:**	**0.057**	**m3/sn**	**21.08.2006**
Gözlem süresinde anlık ençok akım	**:**	**38.3**	**m3/sn**	**11.02.2006**
Gözlem süresinde anlık enaz akım	**:**	**0.057**	**m3/sn**	**21.08.2006**

3. Anahtar Eğrisi (Seviyeler cm olarak)

Seviye	Akım	Seviye	Akım	Seviye	Akım	Seviye	Akım
10	0.054	55	2.9	100	19.9	125	30.8
20	0.084	67	7.0	105	22.0	130	33.0
30	0.157	85	13.9	110	24.2	135	35.2
40	0.300	90	15.8	115	26.4	140	37.4
50	1.0	95	17.8	120	28.6	145	39.6

Akımlar 01 Ekim 2005 'den 30 Eylül 2006' a kadar m3/sn olarak

Gün	Ekim	Kasım	Aralık	Ocak	Şubat	Mart	Nisan	Mayıs	Haziran	Temmuz	Ağustos	Eylül
01	0.100	0.120	4.44	4.14	1.92	5.64	2.74	1.21	0.459	0.396	0.106	0.078
02	0.148	0.111	4.44	3.30	2.20	5.34	2.74	1.05	0.459	0.369	0.111	0.078
03	0.106	0.120	4.44	2.74	1.92	4.74	2.74	0.884	0.459	1.21	0.106	0.078
04	0.106	0.111	4.44	2.47	1.92	4.44	2.74	0.884	0.459	1.36	0.100	0.078
05	0.106	0.106	4.44	2.47	1.92	3.86	2.74	0.884	0.427	1.00	0.100	0.075
06	0.106	0.106	4.44	3.02	5.94	3.58	2.47	0.718	0.459	0.710	0.095	0.075
07	0.106	0.106	4.74	3.02	6.84	3.86	2.47	0.884	0.459	0.710	0.095	0.075
08	0.106	0.106	4.44	2.74	5.04	6.24	2.47	0.884	0.459	0.710	0.095	0.078
09	0.100	0.120	3.86	2.74	4.44	5.94	2.47	1.05	0.459	0.516	0.100	0.075
10	0.106	0.120	3.86	2.74	8.10	5.34	1.92	0.884	0.459	0.516	0.106	0.075
11	0.095	0.111	3.86	1.92	23.3	4.44	1.92	0.553	0.459	0.516	0.100	0.075
12	0.100	0.106	3.58	1.65	14.3	6.54	1.92	0.553	0.459	0.516	0.095	0.078
13	0.106	0.111	3.58	1.65	9.74	7.14	1.92	0.553	0.490	0.516	0.084	0.078
14	0.106	0.111	3.02	1.21	7.78	9.07	2.20	0.553	0.490	0.473	0.069	0.078
15	0.106	0.106	3.02	1.05	6.54	7.78	1.92	0.522	0.553	0.473	0.069	0.078
16	0.111	0.106	2.47	1.05	5.34	6.84	1.92	0.522	0.459	0.430	0.072	0.078
17	0.111	0.111	2.47	1.05	5.34	5.94	1.92	0.522	0.427	0.430	0.069	0.078
18	0.106	0.806	2.74	1.05	5.64	5.34	1.65	0.522	0.396	0.343	0.072	0.078
19	0.157	0.473	5.64	3.86	6.24	4.74	1.38	0.522	0.247	0.260	0.069	0.078
20	0.191	2.74	4.44	6.54	5.94	4.44	1.38	0.553	0.315	0.240	0.069	0.078
21	0.183	0.553	4.44	4.14	5.34	4.14	1.38	0.553	0.427	0.129	0.057	0.078
22	0.148	0.342	4.44	3.58	5.34	4.14	1.38	0.553	0.396	0.129	0.078	0.084
23	0.106	0.261	2.74	3.58	4.44	3.58	1.38	0.553	0.369	0.129	0.078	0.078
24	0.111	0.369	1.05	3.58	4.44	4.14	1.21	0.553	0.342	0.139	0.078	0.100
25	0.111	1.92	1.05	3.58	5.64	3.86	1.05	0.553	0.315	0.120	0.078	0.139
26	0.120	9.07	0.718	2.74	6.24	3.58	1.05	0.553	0.315	0.111	0.078	0.120
27	0.111	5.64	0.553	2.74	6.24	3.58	0.884	0.553	1.05	0.111	0.078	0.100
28	0.106	4.74	0.553	2.74	5.64	3.58	0.884	0.522	0.553	0.111	0.078	0.100
29	0.106	4.44	1.38	2.74	-----	3.30	0.884	0.522	0.522	0.111	0.078	0.174
30	0.106	4.44	1.38	2.20	-----	3.58	0.884	0.490	0.522	0.111	0.075	0.183
31	0.106	-----	3.58	1.92	-----	3.30	-----	0.490	-----	0.106	0.075	-----
Maks.	0.260	16.2	8.42	11.4	38.3	10.4	3.58	4.74	6.84	1.36	0.111	3.25
Min.	0.089	0.106	0.553	1.05	1.92	2.74	0.884	0.459	0.203	0.100	0.057	0.072
Ortalama	0.116	1.26	3.23	2.71	6.20	4.90	1.82	0.665	0.455	0.419	0.084	0.090
LT/SN/Km2	1.17	12.7	32.8	27.5	62.9	49.7	18.5	6.74	4.62	4.25	0.854	0.912
AKIM mm.	3.15	33.0	87.8	73.5	152.	133.	47.8	18.0	12.0	11.4	2.29	2.36
MİL. M3	0.310	3.26	8.66	7.25	15.0	13.1	4.72	1.78	1.18	1.12	0.226	0.233

SU YILI (2006) YILLIK TOPLAM AKIM 56.84 MİLYON M3 576 MM. 18.3 LT/SN/Km2

05. Gediz Havzasi

D05A063 ARMUTLU D. ARMUTLU

YERİ : **KEMALPAŞANIN ARMUTLU BELDESİNDEN MENBAĞA DOĞRU 2.5 KM SONRA DERE ÜZERİNDEDİR. L18**

27°32'5" Doğu - 38°22'25" Kuzey

YAĞIŞ ALANI : **43,50 km2** **YAKLAŞIK KOT : 198 m**

GÖZLEM SÜRESİ : **01.01.2004 - 30.09.2006**

ORTALAMA AKIMLAR : **Gözlem süresinde 0.481 m3/sn. (2 Yıllık) 2006 Su yılında 0.561 m3/sn.**

ANLIK EN ÇOK VE EN AZ AKIMLAR:

2006 Su yılında anlık ençok akım	**:**	**29.8**	**m3/sn**	**11.03.2006**
2006 Su yılında anlık enaz akım	**:**	**0.033**	**m3/sn**	**01.10.2005**
Gözlem süresinde anlık ençok akım	**:**	**29.8**	**m3/sn**	**11.03.2006**
Gözlem süresinde anlık enaz akım	**:**	**0.003**	**m3/sn**	**05.07.2005**

5. Anahtar Eğrisi (Seviyeler cm olarak)

Seviye	Akım	Seviye	Akım	Seviye	Akım	Seviye	Akım
1	0.002	15	0.130	50	2.6	100	13.9
3	0.007	25	0.550	60	3.8	110	17.0
5	0.016	30	0.830	70	6.1	130	23.3
7	0.030	35	1.2	80	8.4	150	30.5
9	0.047	40	1.6	90	11.0	170	37.4

Akımlar 01 Ekim 2005 'den 30 Eylül 2006' a kadar m3/sn olarak

Gün	Ekim	Kasım	Aralık	Ocak	Şubat	Mart	Nisan	Mayıs	Haziran	Temmuz	Ağustos	Eylül
01	0.033	0.043	0.149	0.902	0.539	1.64	0.568	0.254	0.171	0.115	0.068	0.053
02	0.110	0.043	0.149	0.601	0.539	1.43	0.568	0.254	0.171	0.115	0.068	0.053
03	0.055	0.043	0.123	0.539	0.601	1.43	0.511	0.254	0.171	0.115	0.068	0.053
04	0.055	0.055	0.123	0.417	0.601	1.43	0.568	0.254	0.171	0.115	0.068	0.053
05	0.043	0.055	0.123	0.383	0.662	1.43	0.511	0.254	0.171	0.097	0.068	0.053
06	0.033	0.055	0.123	0.417	5.19	1.04	0.454	0.254	0.171	0.097	0.068	0.053
07	0.033	0.055	0.110	0.478	3.50	1.64	0.454	0.254	0.171	0.097	0.068	0.053
08	0.033	0.055	0.110	0.539	2.06	6.78	0.454	0.254	0.171	0.097	0.068	0.053
09	0.033	0.055	0.200	0.478	1.64	3.83	0.414	0.254	0.171	0.097	0.068	0.053
10	0.033	0.055	0.149	0.417	4.73	2.50	0.414	0.254	0.171	0.097	0.068	0.053
11	0.033	0.055	0.149	0.383	11.9	3.50	0.414	0.254	0.171	0.097	0.068	0.053
12	0.033	0.055	0.123	0.348	5.41	10.5	0.374	0.254	0.171	0.097	0.068	0.053
13	0.033	0.055	0.123	0.348	3.17	9.19	0.374	0.226	0.198	0.097	0.068	0.053
14	0.033	0.055	0.123	0.348	2.17	6.78	0.374	0.226	0.198	0.097	0.068	0.053
15	0.033	0.055	0.123	0.348	1.75	4.28	0.374	0.171	0.198	0.097	0.068	0.053
16	0.033	0.055	0.149	0.314	1.53	3.17	0.334	0.171	0.198	0.097	0.068	0.053
17	0.033	0.068	0.123	0.314	1.32	2.34	0.334	0.171	0.198	0.097	0.053	0.053
18	0.033	0.295	0.225	0.279	1.32	2.17	0.334	0.171	0.198	0.097	0.053	0.053
19	0.033	0.225	1.66	0.539	1.43	1.96	0.294	0.171	0.143	0.097	0.053	0.053
20	0.033	0.383	0.813	1.35	1.22	1.85	0.294	0.171	0.115	0.097	0.053	0.053
21	0.033	0.149	0.539	0.813	1.04	1.75	0.254	0.171	0.115	0.097	0.053	0.053
22	0.033	0.123	0.383	0.662	1.04	1.75	0.254	0.171	0.097	0.097	0.053	0.053
23	0.033	0.123	0.348	0.813	0.962	1.64	0.254	0.171	0.097	0.097	0.053	0.053
24	0.033	0.174	0.348	0.813	0.887	1.22	0.254	0.171	0.097	0.097	0.053	0.053
25	0.033	0.251	0.314	0.723	1.64	0.887	0.226	0.171	0.097	0.097	0.053	0.097
26	0.033	1.01	0.279	0.601	2.67	0.813	0.226	0.171	0.097	0.097	0.053	0.097
27	0.033	0.607	0.279	0.601	2.83	0.739	0.254	0.171	0.097	0.097	0.053	0.068
28	0.033	0.295	0.279	0.539	1.96	0.682	0.254	0.171	0.097	0.068	0.053	0.068
29	0.033	0.200	0.314	0.478	-----	0.625	0.254	0.171	0.143	0.068	0.053	0.068
30	0.033	0.174	0.348	0.478	-----	0.568	0.254	0.171	0.143	0.068	0.053	0.068
31	0.033	-----	0.723	0.478	-----	0.568	-----	0.171	-----	0.068	0.053	-----
Maks.	0.675	2.98	3.16	2.52	17.3	29.8	0.887	0.374	0.454	0.143	0.068	0.254
Min.	0.033	0.043	0.110	0.279	0.539	0.568	0.198	0.115	0.053	0.033	0.053	0.053
Ortalama	0.037	0.164	0.294	0.540	2.30	2.58	0.363	0.207	0.153	0.096	0.061	0.058
LT/SN/Km2	0.856	3.77	6.77	12.4	52.8	59.4	8.35	4.75	3.51	2.20	1.40	1.33
AKIM mm.	2.29	9.77	18.1	33.3	128.	159.	21.6	12.7	9.09	5.89	3.74	3.45
MİL. M3	0.100	0.425	0.788	1.45	5.56	6.92	0.942	0.554	0.396	0.256	0.163	0.150

SU YILI (2006) YILLIK TOPLAM AKIM 17.70 MİLYON M3 407 MM. 12.9 LT/SN/Km2

05. Gediz Havzasi

D05A064 DİKEN D. SARIBURUN

YERİ : **UŞAK'DAN GEDİZ'E AYRILAN YOLUN 13 KM SİNDEN SONRA SAĞA AYRILAN KÖY YOLUNUN 12. KM SİNDE SARIDERE KÖYÜNDEDİR.K22**
31°17'59" Doğu - 38°47'6" Kuzey

YAĞIŞ ALANI : **153,80 km2** **YAKLAŞIK KOT : 635 m**

GÖZLEM SÜRESİ : **01.01.2005 - 30.09.2006**

ORTALAMA AKIMLAR : **Gözlem süresinde 0.414 m3/sn. (1 Yıllık) 2006 Su yılında 0.414 m3/sn.**

ANLIK EN ÇOK VE EN AZ AKIMLAR:

2006 Su yılında anlık ençok akım	:	**9.80**	**m3/sn**	**11.02.2006**
2006 Su yılında anlık enaz akım	:	**0.000**	**m3/sn**	**01.10.2005**
Gözlem süresinde anlık ençok akım	:	**9.80**	**m3/sn**	**11.02.2006**
Gözlem süresinde anlık enaz akım	:	**0.000**	**m3/sn**	**01.10.2005**

3. Anahtar Eğrisi (Seviyeler cm olarak)

Seviye	Akım	Seviye	Akım	Seviye	Akım	Seviye	Akım
1	0.000	11	0.018	44	2.1	90	8.6
3	0.000	15	0.082	50	2.8	100	11.0
5	0.000	25	0.540	60	3.9	110	13.2
7	0.001	35	1.2	70	5.2	130	20.0
9	0.006	40	1.6	80	6.6	150	27.0

Akımlar 01 Ekim 2005 'den 30 Eylül 2006' a kadar m3/sn olarak

Gün	Ekim	Kasım	Aralık	Ocak	Şubat	Mart	Nisan	Mayıs	Haziran	Temmuz	Ağustos	Eylül
01	KURU	0.048	0.120	0.776	0.150	1.72	0.946	0.212	0.041	0.003	KURU	KURU
02	KURU	0.074	0.120	0.480	0.265	1.58	0.804	0.212	0.041	0.003	KURU	KURU
03	KURU	0.009	0.120	0.372	0.208	2.87	0.738	0.212	0.041	0.003	KURU	KURU
04	KURU	0.009	0.120	0.318	0.110	2.21	0.738	0.481	0.041	0.003	KURU	KURU
05	KURU	0.009	0.088	0.318	0.110	1.65	0.738	0.422	0.041	0.003	KURU	KURU
06	KURU	0.009	0.088	0.480	1.33	1.49	0.606	0.304	0.041	0.003	KURU	KURU
07	KURU	0.009	0.088	0.372	2.00	1.49	0.540	0.422	0.030	0.003	KURU	KURU
08	KURU	0.009	0.088	0.264	1.21	2.21	0.481	0.422	0.030	0.003	KURU	KURU
09	0.001	0.003	0.057	0.210	0.776	1.99	0.422	0.363	0.030	0.003	KURU	KURU
10	0.003	0.003	0.025	0.210	0.776	1.57	0.481	0.304	0.030	0.003	KURU	KURU
11	0.003	0.009	0.025	0.088	5.62	1.49	0.422	0.245	0.030	0.003	KURU	KURU
12	0.003	0.009	0.025	0.165	4.03	1.57	0.422	0.212	0.030	0.003	KURU	KURU
13	0.003	0.009	0.025	0.088	2.45	1.99	0.363	0.180	0.030	0.003	KURU	KURU
14	0.003	0.009	0.025	0.088	2.27	5.48	0.422	0.180	0.030	0.003	KURU	KURU
15	0.003	0.009	0.025	0.088	2.27	3.21	0.481	0.180	0.030	0.003	KURU	KURU
16	0.009	0.009	0.025	0.088	2.27	2.43	0.363	0.180	0.030	0.003	KURU	KURU
17	0.009	0.009	0.088	0.088	2.27	2.10	0.363	0.180	0.030	0.003	KURU	KURU
18	0.009	0.009	0.088	0.088	2.18	1.76	0.304	0.115	0.030	0.003	KURU	KURU
19	0.009	0.024	1.58	0.554	2.18	1.65	0.481	0.115	0.018	0.003	KURU	KURU
20	0.009	1.06	0.318	1.60	2.27	1.49	1.02	0.147	0.010	0.003	KURU	KURU
21	0.009	0.380	0.165	0.886	1.86	1.49	0.672	0.115	0.010	0.003	KURU	KURU
22	0.009	0.150	0.120	0.798	1.72	1.57	0.672	0.082	0.010	0.003	KURU	KURU
23	0.009	0.074	0.088	0.886	1.58	1.65	0.738	0.082	0.006	0.003	KURU	KURU
24	0.024	0.048	0.088	0.435	1.58	1.76	0.738	0.082	0.003	0.003	KURU	KURU
25	0.024	0.208	0.088	0.435	2.00	1.49	0.245	0.082	0.003	0.003	KURU	KURU
26	0.024	2.09	0.057	0.323	2.00	1.33	0.245	0.082	0.003	0.003	KURU	KURU
27	0.024	0.850	0.057	0.265	1.86	1.25	0.212	0.082	0.003	0.003	KURU	KURU
28	0.024	0.372	0.057	0.265	1.58	1.17	0.212	0.082	0.003	0.003	KURU	KURU
29	0.024	0.210	0.628	0.265	-----	1.10	0.212	0.082	0.003	KURU	KURU	KURU
30	0.024	0.120	0.554	0.265	-----	1.02	0.212	0.062	0.003	KURU	KURU	KURU
31	0.024	-----	0.628	0.150	-----	1.02	-----	0.041	-----	KURU	KURU	-----
Maks.	0.024	3.90	5.48	8.00	9.80	9.80	1.49	4.03	0.304	0.003	KURU	KURU
Min.	KURU	KURU	KURU	0.088	0.110	0.946	0.212	0.041	0.003	KURU	KURU	KURU
Ortalama	0.009	0.195	0.183	0.378	1.75	1.83	0.510	0.192	0.023	0.003	KURU	KURU
LT/SN/Km2	0.059	1.27	1.19	2.46	11.4	11.9	3.31	1.25	0.148	0.018	0.000	0.000
AKIM mm.	0.159	3.28	3.18	6.58	27.5	31.9	8.59	3.35	0.383	0.047	0.000	0.000
MİL. M3	0.024	0.505	0.490	1.01	4.23	4.91	1.32	0.515	0.059	0.007	0.000	0.000

SU YILI (2006) YILLIK TOPLAM AKIM 13.07 MİLYON M3 85 MM. 2.7 LT/SN/Km2

05. Gediz Havzasi

D05A065 GEÇTİN D. DOGANPINAR

YERİ : **GUNESLİ DOGANPINAR KÖYÜNDEN SONRA 1.5 KM SONRA DERE ÜZERİNDEDIR. J20-C3**
29°27'0" Doğu - 39°3'24" Kuzey

YAĞIŞ ALANI : **59,50 km2** **YAKLAŞIK KOT : 787 m**

GÖZLEM SÜRESİ : **01.01.2005 - 30.09.2006**

ORTALAMA AKIMLAR : **Gözlem süresinde 0.688 m3/sn. (1 Yıllık) 2006 Su yılında 0.688 m3/sn.**

ANLIK EN ÇOK VE EN AZ AKIMLAR:

2006 Su yılında anlık encok akım	**:**	**33.7**	**m3/sn**	**12.03.2006**
2006 Su yılında anlık enaz akım	**:**	**0.000**	**m3/sn**	**30.06.2006**
Gözlem süresinde anlık encok akım	**:**	**33.7**	**m3/sn**	**12.03.2006**
Gözlem süresinde anlık enaz akım	**:**	**0.000**	**m3/sn**	**30.06.2006**

3. Anahtar Eğrisi (Seviyeler cm olarak)

Akımlar 01 Ekim 2005 'den 30 Eylül 2006' a kadar m3/sn olarak

Gün	Ekim	Kasım	Aralık	Ocak	Şubat	Mart	Nisan	Mayıs	Haziran	Temmuz	Ağustos	Eylül
01	0.013	0.024	0.220	1.90	0.299	3.50	0.992	0.255	0.018	KURU	KURU	KURU
02	0.017	0.024	0.175	1.23	0.387	2.40	0.874	0.211	0.018	KURU	KURU	KURU
03	0.017	0.030	0.130	1.01	0.387	6.30	0.874	0.166	0.011	KURU	KURU	KURU
04	0.017	0.030	0.116	0.871	0.387	3.10	0.874	0.211	0.011	KURU	KURU	KURU
05	0.017	0.050	0.116	1.09	0.432	2.12	0.874	0.211	0.011	KURU	KURU	KURU
06	0.017	0.050	0.116	1.23	4.50	1.70	0.756	0.166	0.011	KURU	KURU	KURU
07	0.017	0.069	0.103	1.30	2.82	2.26	0.756	0.166	0.011	KURU	KURU	KURU
08	0.017	0.089	0.116	1.01	1.98	4.90	0.756	0.166	0.011	KURU	KURU	KURU
09	0.017	0.030	0.366	0.800	1.46	2.54	0.756	0.166	0.011	KURU	KURU	KURU
10	0.017	0.017	0.175	0.657	5.10	1.98	0.756	0.078	0.011	KURU	KURU	KURU
11	0.017	0.017	0.130	0.585	13.9	2.96	0.756	0.064	0.011	KURU	KURU	KURU
12	0.017	0.017	0.116	0.512	5.10	12.6	0.756	0.064	0.011	KURU	KURU	KURU
13	0.013	0.017	0.116	0.512	2.82	6.30	0.756	0.064	0.011	KURU	KURU	KURU
14	0.013	0.017	0.103	0.512	1.98	11.0	0.432	0.064	0.011	KURU	KURU	KURU
15	0.013	0.017	0.116	0.512	1.46	5.90	0.122	0.051	0.011	KURU	KURU	KURU
16	0.013	0.017	0.293	0.366	1.11	4.50	0.064	0.051	0.011	KURU	KURU	KURU
17	0.013	0.024	0.585	0.175	0.874	3.70	0.051	0.051	0.011	KURU	KURU	KURU
18	0.013	0.366	1.16	0.130	2.26	3.70	0.051	0.051	0.011	KURU	KURU	KURU
19	0.013	0.103	4.10	2.12	2.54	2.96	0.037	0.051	0.003	KURU	KURU	KURU
20	0.013	0.366	1.23	2.82	2.54	2.68	0.037	0.051	0.003	KURU	KURU	KURU
21	0.013	0.116	0.800	1.23	2.26	2.40	0.037	0.037	0.003	KURU	KURU	KURU
22	0.017	0.089	0.585	0.756	1.98	2.12	0.037	0.037	0.001	KURU	KURU	KURU
23	0.017	0.069	0.512	1.35	1.70	1.84	0.037	0.037	0.031	KURU	KURU	KURU
24	0.017	0.069	0.439	0.638	1.70	1.84	0.031	0.031	2.68	KURU	KURU	KURU
25	0.017	0.439	0.366	0.520	4.70	1.70	0.078	0.031	0.520	KURU	KURU	KURU
26	0.017	1.54	0.293	0.432	4.50	1.46	0.211	0.031	0.299	KURU	KURU	KURU
27	0.013	1.42	0.366	0.432	4.90	1.35	0.166	0.031	0.011	KURU	KURU	KURU
28	0.013	0.657	0.512	0.387	3.10	1.23	0.166	0.031	0.003	KURU	KURU	KURU
29	0.013	0.366	0.943	0.343	-----	1.11	0.211	0.024	0.003	KURU	KURU	KURU
30	0.017	0.293	0.657	0.343	-----	0.992	0.211	0.018	KURU	KURU	KURU	KURU
31	0.024	-----	2.82	0.299	-----	0.992	-----	0.018	-----	KURU	KURU	-----
Maks.	0.512	4.78	9.72	26.1	22.8	33.7	1.11	0.343	2.82	KURU	KURU	2.82
Min.	0.013	0.017	0.103	0.116	0.211	0.992	0.031	0.018	KURU	KURU	KURU	KURU
Ortalama	0.016	0.214	0.577	0.841	2.76	3.36	0.417	0.087	0.126	KURU	KURU	KURU
LT/SN/Km2	0.261	3.60	9.69	14.1	46.3	56.5	7.01	1.46	2.11	0.000	0.000	0.000
AKIM mm.	0.700	9.34	26.0	37.9	112.	151.	18.2	3.90	5.47	0.000	0.000	0.000
MİL. M3	0.042	0.556	1.54	2.25	6.67	9.00	1.08	0.232	0.326	0.000	0.000	0.000

SU YILI (2006) YILLIK TOPLAM AKIM 21.70 MİLYON M3 365 MM. 11.6 LT/SN/Km2

05. Gediz Havzasi

D05A066 SELENDİ Ç. SELENDİ

YERİ : **KULA UŞAK KARAYOLUNDA SELENDİ YOLUNDAN SAPILIR KASABA İÇİNDEKİ KÖPRÜDEDİR. K 21 29°52'12" Doğu - 38°43'43" Kuzey**

YAĞIŞ ALANI : **519,40 km2** **YAKLAŞIK KOT : 430 m**

GÖZLEM SÜRESİ : **01.01.2005 - 30.09.2006**

ORTALAMA AKIMLAR : **Gözlem süresinde 2.166 m3/sn. (1 Yıllık) 2006 Su yılında 2.166 m3/sn.**

ANLIK EN ÇOK VE EN AZ AKIMLAR:

2006 Su yılında anlık ençok akım	:	**87.5**	**m3/sn**	**11.02.2006**
2006 Su yılında anlık enaz akım	:	**0.000**	**m3/sn**	**14.10.2005**
Gözlem süresinde anlık ençok akım	:	**87.5**	**m3/sn**	**11.02.2006**
Gözlem süresinde anlık enaz akım	:	**0.000**	**m3/sn**	**14.10.2005**

2. Anahtar Eğrisi (Seviyeler cm olarak)

Seviye	Akım	Seviye	Akım	Seviye	Akım	Seviye	Akım
2	0.000	12	0.007	35	3.0	80	22.4
4	0.000	14	0.028	40	5.2	90	26.8
6	0.000	18	0.133	50	9.2	100	33.0
8	0.000	22	0.398	60	13.6	150	66.5
10	0.001	27	1.0	70	18.0	200	104.

Akımlar 01 Ekim 2005 'den 30 Eylül 2006' a kadar m3/sn olarak

Gün	Ekim	Kasım	Aralık	Ocak	Şubat	Mart	Nisan	Mayıs	Haziran	Temmuz	Ağustos	Eylül
01	KURU	KURU	3.17	5.92	KURU	4.34	2.64	1.05	0.327	0.090	0.047	0.047
02	KURU	KURU	3.53	2.80	KURU	2.48	2.90	1.05	0.261	0.090	0.047	0.015
03	KURU	KURU	3.90	1.70	KURU	9.64	2.64	1.05	0.261	0.483	0.047	0.007
04	0.034	KURU	3.53	0.400	KURU	8.00	2.64	0.937	0.261	1.17	0.076	0.007
05	0.034	KURU	3.53	1.05	KURU	4.77	2.64	2.13	0.261	0.704	0.047	0.007
06	0.034	KURU	3.17	2.43	12.3	2.76	2.13	1.36	0.156	4.13	0.076	0.003
07	KURU	KURU	0.400	1.05	13.4	1.62	1.94	1.17	0.156	7.60	0.076	0.003
08	KURU	KURU	KURU	0.217	8.78	22.4	1.94	2.13	0.156	2.76	0.076	0.003
09	KURU	KURU	KURU	0.034	7.96	15.8	1.94	2.13	0.156	0.483	0.076	0.003
10	KURU	0.400	KURU	0.034	11.1	11.8	1.94	1.55	0.156	0.398	0.076	0.003
11	KURU	0.400	KURU	0.034	63.8	11.4	1.94	1.55	0.156	0.398	0.076	0.003
12	KURU	1.05	KURU	0.034	29.3	11.8	1.94	1.36	0.156	0.398	0.076	0.007
13	KURU	1.70	KURU	0.034	5.20	12.3	1.55	1.75	0.205	0.104	0.076	0.007
14	KURU	2.07	KURU	0.034	3.05	25.5	1.55	1.36	0.205	0.104	0.076	0.003
15	KURU	2.43	KURU	0.034	2.76	14.0	1.75	1.05	0.205	0.076	0.076	0.028
16	KURU	2.43	KURU	KURU	2.76	11.4	1.55	3.77	0.205	0.076	0.047	0.047
17	KURU	2.80	KURU	KURU	2.76	9.64	1.55	1.55	0.156	0.076	0.047	0.003
18	KURU	3.17	KURU	KURU	2.76	8.80	1.36	1.05	0.156	0.076	0.076	0.015
19	KURU	2.80	5.52	9.59	3.48	9.20	1.36	1.05	0.156	0.076	0.047	0.015
20	KURU	5.11	2.43	18.0	7.60	8.00	1.36	0.937	0.118	0.076	0.047	0.007
21	KURU	2.80	0.217	11.1	7.60	7.20	1.05	0.820	0.118	0.076	0.047	0.001
22	KURU	1.70	KURU	10.6	6.40	6.00	1.36	0.704	0.118	0.076	0.047	KURU
23	KURU	1.05	KURU	8.78	5.20	5.60	2.13	0.704	0.118	0.076	0.047	0.001
24	KURU	1.05	KURU	2.80	4.77	5.60	1.75	0.587	0.118	0.047	0.047	0.076
25	KURU	3.53	KURU	1.70	4.77	5.20	1.36	0.483	0.118	0.047	0.047	0.612
26	KURU	20.4	KURU	1.05	5.20	4.48	1.17	0.327	0.118	0.047	0.047	0.257
27	KURU	7.55	KURU	KURU	7.20	3.77	1.05	0.327	0.118	0.047	0.047	0.257
28	KURU	3.90	KURU	KURU	6.00	3.15	1.05	0.327	0.090	0.047	0.047	0.257
29	KURU	3.17	1.05	KURU	-----	3.77	1.05	0.327	0.118	0.047	0.047	1.21
30	KURU	3.17	1.05	KURU	-----	3.15	1.05	0.327	0.090	0.133	0.028	2.19
31	KURU	-----	7.15	KURU	-----	2.39	-----	0.327	-----	0.133	0.028	-----
Maks.	0.034	36.4	18.0	71.8	87.5	47.7	4.84	12.3	10.5	20.6	0.742	12.3
Min.	KURU	KURU	KURU	KURU	KURU	1.62	0.587	0.327	0.065	0.028	0.015	KURU
Ortalama	0.003	2.42	1.25	2.56	8.01	8.26	1.74	1.14	0.166	0.650	0.057	0.170
LT/SN/Km2	0.006	4.66	2.40	4.93	15.4	15.9	3.36	2.19	0.320	1.25	0.110	0.327
AKIM mm.	0.017	12.1	6.43	13.2	37.3	42.6	8.70	5.86	0.831	3.35	0.294	0.847
MİL. M3	0.009	6.28	3.34	6.86	19.4	22.1	4.52	3.05	0.431	1.74	0.153	0.440

SU YILI (2006) YILLIK TOPLAM AKIM 68.32 MİLYON M3 132 MM. 4.2 LT/SN/Km2

05. Gediz Havzasi

D05A067 İMREN D. ULUCAK

YERİ : **KULA UŞAK KARAYOLUNDA SELENDI KAVSAGINDAN SONRAKI KOPRUDEN SAGA SAPILIR 1,5KM SONRA DERE UZERINDE**
36°56'57" Doğu - 38°36'43" Kuzey

YAĞIŞ ALANI : **371,60 km2** **YAKLAŞIK KOT : 463 m**

GÖZLEM SÜRESİ : **01.01.2005 - 30.09.2006**

ORTALAMA AKIMLAR : **Gözlem süresinde 0.296 m3/sn. (1 Yıllık) 2006 Su yılında 0.296 m3/sn.**

ANLIK EN ÇOK VE EN AZ AKIMLAR:

2006 Su yılında anlık ençok akım	:	**23.0**	**m3/sn**	**14.03.2006**
2006 Su yılında anlık enaz akım	:	**0.000**	**m3/sn**	**01.10.2005**
Gözlem süresinde anlık ençok akım	:	**23.0**	**m3/sn**	**14.03.2006**
Gözlem süresinde anlık enaz akım	:	**0.000**	**m3/sn**	**01.10.2005**

1. Anahtar Eğrisi (Seviyeler cm olarak)

Seviye	Akım	Seviye	Akım	Seviye	Akım	Seviye	Akım
20	0.000	35	0.000	100	10.6	150	32.0
23	0.000	38	0.000	110	15.0	160	37.5
26	0.000	41	0.000	120	19.0	170	43.0
29	0.000	44	0.001	130	23.0	200	60.0
32	0.000	70	2.4	140	27.5	210	66.0

Akımlar 01 Ekim 2005 'den 30 Eylül 2006' a kadar m3/sn olarak

Gün	Ekim	Kasım	Aralık	Ocak	Şubat	Mart	Nisan	Mayıs	Haziran	Temmuz	Ağustos	Eylül
01	KURU	0.001	0.047	0.071	0.071	1.70	0.398	0.071	KURU	KURU	KURU	KURU
02	KURU	0.001	0.047	0.071	0.117	0.828	0.312	0.071	KURU	KURU	KURU	KURU
03	0.001	0.001	0.047	0.071	0.484	0.656	0.312	0.071	KURU	KURU	KURU	KURU
04	0.001	0.001	0.047	0.047	0.570	0.570	0.312	0.071	KURU	KURU	KURU	KURU
05	0.001	0.001	0.047	0.071	0.398	0.398	0.570	0.047	KURU	KURU	KURU	KURU
06	0.001	0.001	0.047	0.071	1.28	0.398	0.312	0.047	KURU	KURU	KURU	KURU
07	0.001	0.001	0.047	0.094	3.30	0.312	0.140	0.047	KURU	KURU	KURU	KURU
08	0.001	0.001	0.047	0.094	2.12	1.28	0.226	0.047	KURU	KURU	KURU	KURU
09	KURU	0.001	0.047	0.071	1.70	2.94	0.312	0.047	KURU	KURU	KURU	KURU
10	KURU	0.001	0.047	0.071	1.14	1.70	0.570	0.024	KURU	KURU	KURU	KURU
11	KURU	0.001	0.047	0.047	4.80	1.00	0.312	0.024	KURU	KURU	KURU	KURU
12	KURU	0.001	0.047	0.047	9.92	0.914	0.226	0.024	KURU	KURU	KURU	KURU
13	KURU	0.001	0.047	0.047	3.66	1.70	0.140	0.024	0.117	KURU	KURU	KURU
14	0.001	0.001	0.047	0.047	1.84	9.92	0.140	0.024	0.047	KURU	KURU	KURU
15	0.001	0.001	0.047	0.047	1.14	5.60	0.140	0.024	0.001	KURU	KURU	KURU
16	0.001	0.001	0.047	0.047	0.742	2.63	0.140	0.024	0.001	KURU	KURU	KURU
17	0.001	0.001	0.047	0.047	0.656	1.26	0.140	0.024	0.001	KURU	KURU	KURU
18	0.001	0.024	0.047	0.047	0.570	1.11	0.140	0.024	KURU	KURU	KURU	KURU
19	0.001	0.001	0.140	0.047	0.656	2.63	0.140	0.024	KURU	KURU	KURU	KURU
20	0.001	0.024	0.398	0.484	0.656	2.12	0.094	0.024	KURU	KURU	KURU	KURU
21	0.001	0.024	0.117	0.312	0.828	1.84	0.094	0.024	0.001	KURU	KURU	KURU
22	0.001	0.001	0.117	0.140	0.656	1.42	0.094	0.024	0.001	KURU	KURU	KURU
23	0.001	0.047	0.071	0.398	0.484	1.14	0.117	0.024	KURU	KURU	KURU	KURU
24	0.001	0.047	0.071	0.656	0.398	0.914	0.117	0.024	KURU	KURU	KURU	KURU
25	0.001	0.071	0.071	0.484	0.398	0.828	0.117	0.001	KURU	KURU	KURU	KURU
26	0.001	2.40	0.047	0.398	0.398	0.828	0.094	KURU	KURU	KURU	KURU	KURU
27	0.001	0.484	0.047	0.226	1.56	0.656	0.071	KURU	KURU	KURU	KURU	KURU
28	0.001	0.117	0.047	0.140	1.00	0.570	0.071	KURU	KURU	KURU	KURU	KURU
29	KURU	0.094	0.071	0.117	-----	0.484	0.071	KURU	KURU	KURU	KURU	KURU
30	0.001	0.071	0.094	0.094	-----	0.398	0.071	KURU	KURU	KURU	KURU	KURU
31	0.001	-----	0.094	0.047	-----	0.398	-----	KURU	-----	KURU	KURU	-----
Maks.	0.047	6.00	0.914	1.28	14.1	23.0	2.12	0.071	5.70	KURU	KURU	KURU
Min.	KURU	0.001	0.024	KURU	KURU	0.312	0.071	KURU	KURU	KURU	KURU	KURU
Ortalama	0.001	0.114	0.072	0.150	1.48	1.59	0.200	0.028	0.006	KURU	KURU	KURU
LT/SN/Km2	0.002	0.307	0.194	0.404	3.99	4.27	0.538	0.076	0.015	0.000	0.000	0.000
AKIM mm.	0.005	0.796	0.519	1.08	9.66	11.4	1.39	0.205	0.039	0.000	0.000	0.000
MİL. M3	0.002	0.296	0.193	0.402	3.59	4.25	0.518	0.076	0.015	0.000	0.000	0.000

SU YILI (2006) YILLIK TOPLAM AKIM 9.34 MİLYON M3 25 MM. 0.8 LT/SN/Km2

06

KÜÇÜK MENDERES HAVZASI

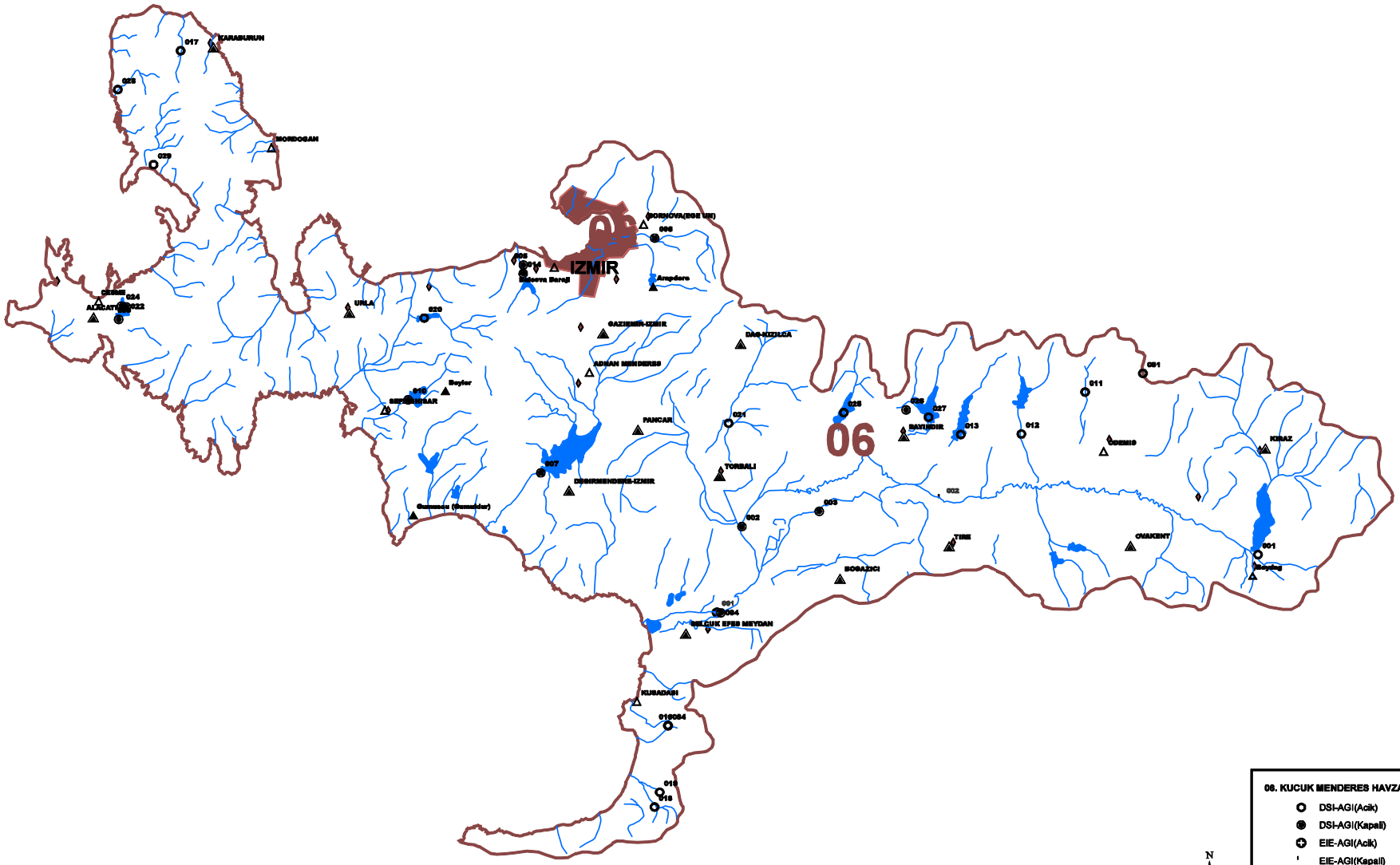
06
IZMIR
KARABURUN
BORDOGAN
DEMIRE
ALACATI
URLA
Seyfer
GAZIEMIR-IZMIR
ADNAN MENDERES
DAG-KIZILCA
PANCAR
TORBALI
DEMIRMENDERES-IZNIR
Gumuse (Kemalpa)
BAYINDIR
DEMIRCI
KIRAZ
TIRE
OVAKENT
BOGAZICI
SELCUK EFES MEYDAN
KUSADASI
Bayindir
Araplarce
Gebeve Baraji
(SORKOVA(EGE UN)
1:500.000
N
06. KUCUK MENDERES HAVZASI
DSI-AGI(Acik)
DSI-AGI(Kapali)
EIE-AGI(Acik)
EIE-AGI(Kapali)
DSI-MGI(Acik)
DSI-MGI(Kapali)
DMI-MGI(Acik)
DMI-MGI(Kapali)

06. Küçük Menderes Havzasi

D06A011 RAHMANLAR Ç. BEBEKLER

YERİ : ÖDEMİŞ BEBEKLER KÖY YOLUNU TAKİBEN BEBEKLERE VARILIR İSTASYON BEBEKLERDEDİR.(PAFTA L19-B3)
27°55'41" Doğu - 38°17'18" Kuzey

YAĞIŞ ALANI : 37,00 km2 **YAKLAŞIK KOT** : 220 m

GÖZLEM SÜRESİ : 01.10.1979 - 30.09.2006

ORTALAMA AKIMLAR : Gözlem süresinde 0.398 m3/sn. (26 Yıllık) 2006 Su yılında 0.423 m3/sn.

ANLIK EN ÇOK VE EN AZ AKIMLAR:

2006 Su yılında anlık ençok akım	:	6.62	m3/sn	06.02.2006
2006 Su yılında anlık enaz akım	:	0.000	m3/sn	28.05.2006
Gözlem süresinde anlık ençok akım	:	44.4	m3/sn	05.12.1981
Gözlem süresinde anlık enaz akım	:	0.000	m3/sn	01.10.1979

8. Anahtar Eğrisi (Seviyeler cm olarak)

Seviye	Akım	Seviye	Akım	Seviye	Akım	Seviye	Akım
1	0.000	11	0.000	45	2.1	70	6.6
3	0.000	13	0.000	50	2.7	75	8.0
5	0.000	15	0.003	55	3.5	80	9.2
7	0.000	25	0.250	60	4.4	90	12.5
9	0.000	35	0.960	65	5.6	100	16.5

Akımlar 01 Ekim 2005 'den 30 Eylül 2006' a kadar m3/sn olarak

Gün	Ekim	Kasım	Aralık	Ocak	Şubat	Mart	Nisan	Mayıs	Haziran	Temmuz	Ağustos	Eylül
01	0.001	0.001	0.212	0.971	0.780	0.971	0.708	0.366	KURU	KURU	KURU	KURU
02	0.001	0.001	0.173	0.861	0.861	0.861	0.708	0.308	KURU	KURU	KURU	KURU
03	0.001	0.002	0.135	0.699	0.780	1.19	0.624	0.308	KURU	KURU	KURU	KURU
04	0.001	0.046	0.135	0.699	0.699	0.971	0.708	0.308	KURU	KURU	KURU	KURU
05	0.001	0.046	0.096	0.780	0.971	0.861	0.708	0.308	KURU	KURU	KURU	KURU
06	0.001	0.046	0.096	0.971	3.79	0.861	0.624	0.250	KURU	KURU	KURU	KURU
07	0.001	0.046	0.058	0.861	2.24	1.30	0.540	0.250	KURU	KURU	KURU	KURU
08	0.001	0.046	0.096	0.861	1.69	2.86	0.540	0.212	KURU	KURU	KURU	0.001
09	0.001	0.046	0.096	0.861	1.30	1.71	0.540	0.212	0.001	KURU	KURU	0.003
10	0.001	0.046	0.058	0.780	3.23	1.16	0.540	0.173	0.001	KURU	KURU	KURU
11	0.001	0.046	0.058	0.699	4.67	1.58	0.540	0.173	0.001	KURU	KURU	KURU
12	0.001	0.046	0.047	0.699	3.94	3.18	0.482	0.173	0.001	KURU	KURU	KURU
13	0.002	0.046	0.036	0.618	2.82	2.70	0.482	0.135	0.001	KURU	KURU	KURU
14	0.002	0.046	0.058	0.618	2.24	3.18	0.540	0.135	KURU	KURU	KURU	KURU
15	0.002	0.046	0.096	0.618	1.82	2.70	0.482	0.135	KURU	KURU	KURU	KURU
16	0.002	0.046	0.096	0.537	1.41	2.10	0.482	0.096	KURU	KURU	KURU	KURU
17	0.002	0.081	0.096	0.290	1.30	1.45	0.482	0.096	KURU	KURU	KURU	KURU
18	0.002	0.624	0.250	0.456	1.19	1.97	0.424	0.058	KURU	KURU	KURU	KURU
19	0.002	0.212	1.45	2.24	1.08	1.58	0.366	0.058	KURU	KURU	KURU	KURU
20	0.001	0.308	1.19	2.39	0.971	1.25	0.366	0.047	KURU	KURU	KURU	KURU
21	0.001	0.173	0.780	1.19	0.861	1.06	0.308	0.047	KURU	KURU	KURU	KURU
22	0.001	0.096	0.618	1.08	0.861	0.960	0.366	0.036	KURU	KURU	KURU	KURU
23	0.001	0.135	0.537	1.08	0.861	0.960	0.366	0.025	KURU	KURU	KURU	KURU
24	0.001	0.212	0.456	1.08	0.861	0.960	0.366	0.025	KURU	KURU	KURU	KURU
25	0.001	0.308	0.456	1.19	1.08	1.06	0.366	0.025	KURU	KURU	KURU	KURU
26	0.001	0.960	0.456	1.08	1.82	0.960	0.308	0.014	KURU	KURU	KURU	KURU
27	0.001	0.624	0.373	0.971	1.55	0.876	0.308	0.014	KURU	KURU	KURU	KURU
28	0.001	0.424	0.456	0.861	1.08	0.792	0.366	0.003	KURU	KURU	KURU	KURU
29	0.001	0.308	0.618	0.861	-----	0.708	0.366	KURU	KURU	KURU	KURU	KURU
30	0.001	0.250	0.537	0.780	-----	0.708	0.366	KURU	KURU	KURU	KURU	KURU
31	0.001	-----	1.30	0.780	-----	0.708	-----	KURU	-----	KURU	KURU	-----
Maks.	0.007	1.25	2.22	3.23	6.62	4.88	0.708	0.366	0.001	KURU	KURU	0.003
Min.	0.001	0.001	0.036	0.290	0.699	0.708	0.308	KURU	KURU	KURU	KURU	KURU
Ortalama	0.001	0.177	0.359	0.918	1.67	1.43	0.479	0.129	0.000	KURU	KURU	0.000
LT/SN/Km2	0.033	4.79	9.69	24.8	45.1	38.5	12.9	3.48	0.005	0.000	0.000	0.004
AKIM mm.	0.089	12.4	26.0	66.5	109.	103.	33.6	9.32	0.012	0.000	0.000	0.009
MİL. M3	0.003	0.459	0.961	2.46	4.04	3.82	1.24	0.345	0.000	0.000	0.000	0.000

SU YILI (2006) YILLIK TOPLAM AKIM 13.33 MİLYON M3 360 MM. 11.4 LT/SN/Km2

06. Küçük Menderes Havzasi

D06A019 ELEKÇİ DERESİ DAVUTLAR

YERİ : **DAVUTLAR-KUŞADASI YOLUNUN 2.KM- SİNDEKİ,ELEKÇİ DERESİ'NİN DAVUTLAR-KUŞADASI KARAYOLUNU KESTİĞİ KÖPRÜDEDİR.**
27°18'3" Doğu - 37°45'0" Kuzey

YAĞIŞ ALANI : **9,10 km2** **YAKLAŞIK KOT : 37 m**

GÖZLEM SÜRESİ : **01.09.1988 - 30.09.2006**

ORTALAMA AKIMLAR : **Gözlem süresinde 0.067 m3/sn. (12 Yıllık) 2006 Su yılında 0.093 m3/sn.**

ANLIK EN ÇOK VE EN AZ AKIMLAR:

2006 Su yılında anlık ençok akım	:	**32.0**	**m3/sn**	**25.11.2005**
2006 Su yılında anlık enaz akım	:	**0.000**	**m3/sn**	**04.10.2005**
Gözlem süresinde anlık ençok akım	:	**42.0**	**m3/sn**	**04.03.1994**
Gözlem süresinde anlık enaz akım	:	**0.000**	**m3/sn**	**01.10.1989**

Akımlar 01 Ekim 2005 'den 30 Eylül 2006' a kadar m3/sn olarak

Gün	Ekim	Kasım	Aralık	Ocak	Şubat	Mart	Nisan	Mayıs	Haziran	Temmuz	Ağustos	Eylül
01	0.001	KURU	0.023	0.100	0.030	0.140	0.085	0.049	0.025	0.004	0.004	0.004
02	0.004	KURU	0.023	0.100	0.030	0.140	0.085	0.049	0.025	0.004	0.004	0.004
03	0.001	KURU	0.023	0.100	0.030	0.180	0.085	0.049	0.025	0.004	0.004	0.004
04	KURU	KURU	0.023	0.100	0.030	0.180	0.085	0.065	0.025	0.004	0.004	0.004
05	KURU	KURU	0.023	0.120	0.030	0.180	0.065	0.065	0.025	0.004	0.004	0.004
06	KURU	KURU	0.023	0.049	0.160	0.180	0.065	0.049	0.025	0.004	0.004	0.004
07	KURU	KURU	0.023	0.049	0.180	0.708	0.065	0.049	0.025	0.004	0.004	0.004
08	KURU	KURU	0.017	0.049	0.140	1.02	0.065	0.049	0.023	0.004	0.004	0.004
09	KURU	KURU	0.017	0.049	0.085	1.11	0.065	0.049	0.023	0.004	0.004	0.004
10	KURU	KURU	0.017	0.049	0.140	1.11	0.065	0.049	0.023	0.004	0.004	0.004
11	KURU	KURU	0.017	0.049	0.312	1.11	0.065	0.049	0.023	0.004	0.004	0.004
12	KURU	KURU	0.017	0.049	0.510	1.20	0.065	0.049	0.017	0.004	0.004	0.004
13	KURU	KURU	0.017	0.049	0.160	1.30	0.065	0.049	0.017	0.004	0.004	0.004
14	KURU	KURU	0.023	0.049	0.160	0.931	0.100	0.049	0.017	0.004	0.004	0.004
15	KURU	KURU	0.065	0.049	0.160	0.774	0.085	0.049	0.017	0.004	0.004	0.004
16	KURU	KURU	0.049	0.049	0.160	0.774	0.085	0.030	0.017	0.004	0.004	0.004
17	KURU	0.002	0.049	0.049	0.160	0.774	0.085	0.030	0.017	0.004	0.004	0.004
18	KURU	KURU	0.030	0.049	0.160	0.774	0.085	0.030	0.017	0.004	0.004	0.004
19	KURU	KURU	0.085	0.100	0.160	0.774	0.085	0.030	0.023	0.004	0.004	0.004
20	KURU	KURU	0.065	0.085	0.120	0.774	0.085	0.030	0.023	0.004	0.004	0.004
21	KURU	KURU	0.030	0.085	0.085	0.312	0.065	0.030	0.017	0.004	0.004	0.004
22	KURU	0.004	0.025	0.065	0.085	0.100	0.065	0.030	0.017	0.004	0.004	0.004
23	KURU	0.002	0.023	0.049	0.085	0.100	0.065	0.030	0.017	0.004	0.004	0.004
24	KURU	0.002	0.025	0.140	0.085	0.100	0.049	0.030	0.017	0.004	0.004	0.004
25	KURU	1.11	0.025	0.120	0.085	0.100	0.049	0.030	0.017	0.004	0.004	0.004
26	KURU	1.98	0.025	0.065	0.120	0.100	0.049	0.030	0.017	0.004	0.004	0.004
27	KURU	1.75	0.049	0.030	0.100	0.100	0.049	0.030	0.004	0.004	0.004	0.004
28	KURU	1.75	0.049	0.030	0.120	0.100	0.049	0.030	0.004	0.004	0.004	0.004
29	KURU	0.708	0.049	0.030	-----	0.100	0.049	0.030	0.004	0.004	0.004	0.023
30	KURU	0.023	0.049	0.030	-----	0.085	0.049	0.030	0.004	0.004	0.004	0.025
31	KURU	-----	0.120	0.030	-----	0.085	-----	0.025	-----	0.004	0.004	-----
Maks.	14.3	32.0	1.20	1.57	2.79	8.86	0.576	0.065	0.025	0.004	0.004	0.378
Min.	KURU	KURU	0.017	0.025	0.030	0.085	0.049	0.025	0.004	0.004	0.004	0.004
Ortalama	0.000	0.244	0.035	0.065	0.132	0.497	0.069	0.040	0.018	0.004	0.004	0.005
LT/SN/Km2	0.021	26.9	3.89	7.15	14.5	54.6	7.59	4.40	2.01	0.440	0.440	0.586
AKIM mm.	0.057	69.6	10.4	19.1	35.0	146.	19.7	11.8	5.22	1.18	1.18	1.52
MİL. M3	0.001	0.633	0.095	0.174	0.318	1.33	0.179	0.107	0.048	0.011	0.011	0.014

SU YILI (2006) YILLIK TOPLAM AKIM 2.92 MİLYON M3 321 MM. 10.2 LT/SN/Km2

06. Küçük Menderes Havzasi

D06A024 GELİNALAN D. SEFERHİSAR

YERİ : **SEFERİHİSARDAN 2 KM SONRA GELİNALAN DERESİNDEDİR.(PAFTA L17-C1)**
26°51'39" Doğu - 38°11'24" Kuzey

YAĞIŞ ALANI : **14,50 km2** **YAKLAŞIK KOT : 60 m**

GÖZLEM SÜRESİ : **01.10.1998 - 30.09.2006**

ORTALAMA AKIMLAR : **Gözlem süresinde 0.101 m3/sn. (4 Yıllık) 2006 Su yılında 0.072 m3/sn.**

ANLIK EN ÇOK VE EN AZ AKIMLAR:

2006 Su yılında anlık ençok akım	:	**3.18**	**m3/sn**	**09.03.2006**
2006 Su yılında anlık enaz akım	:	**0.000**	**m3/sn**	**01.10.2005**
Gözlem süresinde anlık ençok akım	:	**17.0**	**m3/sn**	**22.12.2001**
Gözlem süresinde anlık enaz akım	:	**0.000**	**m3/sn**	**01.10.2000**

7. Anahtar Eğrisi (Seviyeler cm olarak)

Seviye	Akım	Seviye	Akım	Seviye	Akım	Seviye	Akım
20	0.000	120	3.9	160	18.5	270	64.3
40	0.000	130	6.8	170	23.5	280	68.6
78	0.001	133	8.0	200	34.6	290	72.9
90	0.260	140	10.0	230	47.0	300	77.2
110	2.0	150	14.0	260	60.0	330	90.5

Akımlar 01 Ekim 2005 'den 30 Eylül 2006' a kadar m3/sn olarak

Gün	Ekim	Kasım	Aralık	Ocak	Şubat	Mart	Nisan	Mayıs	Haziran	Temmuz	Ağustos	Eylül
01	KURU	KURU	0.018	0.158	0.057	0.025	0.035	0.003	0.003	0.006	KURU	KURU
02	KURU	KURU	0.018	0.108	0.057	0.018	0.035	0.003	0.003	0.006	KURU	KURU
03	KURU	KURU	0.018	0.057	0.057	0.018	0.029	0.003	0.003	0.004	KURU	KURU
04	KURU	KURU	0.004	0.032	0.032	0.018	0.029	0.003	0.003	0.004	KURU	KURU
05	KURU	KURU	0.004	0.032	0.032	0.011	0.023	0.003	0.003	0.004	KURU	KURU
06	KURU	KURU	0.003	0.082	0.235	0.011	0.023	0.003	0.003	0.002	KURU	KURU
07	KURU	KURU	0.003	0.057	0.235	0.133	0.018	0.003	0.003	0.002	KURU	KURU
08	KURU	KURU	0.003	0.032	0.898	1.49	0.018	0.003	0.003	0.001	KURU	KURU
09	KURU	KURU	0.003	0.025	0.442	2.05	0.018	0.003	0.003	0.001	KURU	KURU
10	KURU	KURU	0.003	0.025	0.286	2.30	0.018	0.003	0.003	KURU	KURU	KURU
11	KURU	KURU	0.003	0.018	0.235	1.69	0.014	0.003	0.003	KURU	KURU	KURU
12	KURU	KURU	0.003	0.018	0.183	0.898	0.011	0.003	0.003	KURU	KURU	KURU
13	KURU	KURU	0.003	0.018	0.158	2.30	0.011	0.003	0.003	KURU	KURU	KURU
14	KURU	KURU	0.003	0.018	0.133	2.05	0.018	0.003	0.003	KURU	KURU	KURU
15	KURU	KURU	0.133	0.011	0.108	0.765	0.023	0.003	0.003	KURU	KURU	KURU
16	KURU	KURU	0.108	0.011	0.082	0.579	0.014	0.003	0.003	KURU	KURU	KURU
17	KURU	KURU	0.032	0.004	0.082	0.372	0.014	0.003	0.003	KURU	KURU	KURU
18	KURU	KURU	0.025	0.004	0.082	0.625	0.014	0.003	0.003	KURU	KURU	KURU
19	KURU	KURU	0.032	0.004	0.057	0.452	0.011	0.003	0.003	KURU	KURU	KURU
20	KURU	KURU	0.018	0.004	0.057	0.305	0.011	0.003	0.003	KURU	KURU	KURU
21	KURU	KURU	0.018	0.004	0.057	0.251	0.011	0.003	0.003	KURU	KURU	KURU
22	KURU	KURU	0.018	0.004	0.032	0.197	0.009	0.003	0.004	KURU	KURU	KURU
23	KURU	KURU	0.018	0.018	0.032	0.157	0.009	0.003	0.009	KURU	KURU	KURU
24	KURU	KURU	0.011	0.158	0.025	0.136	0.006	0.003	0.009	KURU	KURU	KURU
25	KURU	KURU	0.011	0.597	0.025	0.116	0.004	0.003	0.009	KURU	KURU	0.002
26	KURU	0.338	0.011	0.183	0.025	0.116	0.004	0.003	0.009	KURU	KURU	0.002
27	KURU	0.597	0.011	0.133	0.025	0.084	0.004	0.003	0.009	KURU	KURU	0.003
28	KURU	0.108	0.018	0.108	0.025	0.084	0.004	0.003	0.009	KURU	KURU	0.004
29	KURU	0.057	0.082	0.108	-----	0.059	0.004	0.003	0.009	KURU	KURU	0.009
30	KURU	0.025	0.057	0.082	-----	0.059	0.003	0.003	0.009	KURU	KURU	0.018
31	KURU	-----	0.545	0.057	-----	0.047	-----	0.003	-----	KURU	KURU	-----
Maks.	KURU	2.30	2.78	2.05	1.81	3.18	0.084	0.003	0.009	0.006	KURU	0.018
Min.	KURU	KURU	0.003	0.004	0.018	0.011	0.003	0.003	0.003	KURU	KURU	KURU
Ortalama	KURU	0.038	0.040	0.070	0.134	0.562	0.015	0.003	0.005	0.001	KURU	0.001
LT/SN/Km2	0.000	2.59	2.75	4.83	9.25	38.7	1.02	0.207	0.320	0.067	0.000	0.087
AKIM mm.	0.000	6.70	7.37	12.9	22.4	104.	2.65	0.554	0.828	0.179	0.000	0.226
MİL. M3	0.000	0.097	0.107	0.187	0.324	1.50	0.038	0.008	0.012	0.003	0.000	0.003

SU YILI (2006) YILLIK TOPLAM AKIM 2.28 MİLYON M3 157 MM. 5.0 LT/SN/Km2

06. Küçük Menderes Havzasi

D06A025 ULADİ Ç. YAKAPINAR

YERİ : **BAYINDIR-YAKAPINAR KÖY YOLUNUN 3.5 KM SİNDEKİ KÖPRÜDEDİR. (PAFTA L19-D1)**
27°33'13" Doğu - 38°14'29" Kuzey

YAĞIŞ ALANI : **69,10 km2** **YAKLAŞIK KOT : 120 m**

GÖZLEM SÜRESİ : **01.10.1996 - 30.09.2006**

ORTALAMA AKIMLAR : **Gözlem süresinde 0.440 m3/sn. (6 Yıllık) 2006 Su yılında 0.481 m3/sn.**

ANLIK EN ÇOK VE EN AZ AKIMLAR:

2006 Su yılında anlık ençok akım	:	**23.9**	**m3/sn**	**11.03.2006**
2006 Su yılında anlık enaz akım	:	**0.010**	**m3/sn**	**08.08.2006**
Gözlem süresinde anlık ençok akım	:	**39.4**	**m3/sn**	**22.12.2001**
Gözlem süresinde anlık enaz akım	:	**0.000**	**m3/sn**	**11.09.2001**

2. Anahtar Eğrisi (Seviyeler cm olarak)

Seviye	Akım	Seviye	Akım	Seviye	Akım	Seviye	Akım
1	0.000	17	0.144	70	5.7	170	26.4
3	0.001	21	0.253	90	8.7	190	31.4
5	0.005	28	0.557	110	12.3	210	36.4
7	0.014	38	1.2	130	16.4	220	38.9
10	0.033	53	3.1	150	21.4	230	41.4

Akımlar 01 Ekim 2005 'den 30 Eylül 2006' a kadar m3/sn olarak

Gün	Ekim	Kasım	Aralık	Ocak	Şubat	Mart	Nisan	Mayıs	Haziran	Temmuz	Ağustos	Eylül
01	0.056	0.125	0.304	0.694	0.355	1.46	0.838	0.404	0.174	0.051	0.039	0.010
02	0.067	0.125	0.304	0.557	0.355	1.25	0.770	0.367	0.174	0.051	0.039	0.010
03	0.086	0.125	0.304	0.456	0.456	1.14	0.643	0.367	0.174	0.051	0.039	0.010
04	0.067	0.125	0.279	0.405	0.456	1.04	0.703	0.367	0.174	0.051	0.039	0.010
05	0.067	0.144	0.279	0.405	0.405	0.905	0.703	0.367	0.196	0.051	0.039	0.010
06	0.056	0.144	0.279	0.355	2.11	0.905	0.643	0.367	0.196	0.051	0.039	0.010
07	0.056	0.144	0.279	0.304	1.62	1.46	0.643	0.367	0.219	0.051	0.039	0.010
08	0.056	0.144	0.279	0.304	0.995	5.23	0.643	0.367	0.196	0.051	0.010	0.010
09	0.056	0.159	0.405	0.304	0.739	2.98	0.583	0.330	0.174	0.051	0.010	0.010
10	0.056	0.159	0.304	0.304	3.91	2.07	0.583	0.330	0.174	0.051	0.010	0.010
11	0.056	0.159	0.304	0.304	8.73	3.24	0.583	0.330	0.151	0.051	0.010	0.010
12	0.067	0.159	0.304	0.304	3.99	6.93	0.583	0.330	0.129	0.051	0.010	0.010
13	0.067	0.190	0.304	0.279	2.38	5.73	0.583	0.293	0.129	0.051	0.010	0.010
14	0.067	0.190	0.304	0.279	1.87	4.61	0.583	0.293	0.129	0.051	0.010	0.010
15	0.067	0.190	0.304	0.279	1.35	3.24	0.524	0.293	0.129	0.051	0.010	0.010
16	0.067	0.190	0.304	0.279	1.25	2.49	0.464	0.293	0.106	0.051	0.010	0.010
17	0.067	0.222	0.304	0.279	1.04	2.17	0.464	0.256	0.106	0.051	0.010	0.010
18	0.086	0.603	0.405	0.279	1.04	1.97	0.464	0.256	0.106	0.051	0.010	0.010
19	0.086	0.456	1.74	0.304	1.04	1.87	0.464	0.256	0.106	0.051	0.010	0.010
20	0.086	0.557	0.506	0.824	0.973	1.56	0.464	0.256	0.106	0.051	0.010	0.010
21	0.086	0.279	0.355	0.456	0.905	1.46	0.404	0.256	0.087	0.051	0.010	0.010
22	0.086	0.190	0.304	0.405	0.838	1.35	0.404	0.256	0.087	0.051	0.010	0.010
23	0.086	0.159	0.279	0.405	0.838	1.25	0.464	0.256	0.087	0.051	0.010	0.010
24	0.086	0.222	0.279	0.405	0.838	1.14	0.404	0.219	0.087	0.051	0.010	0.010
25	0.086	0.304	0.279	0.456	1.25	1.14	0.404	0.219	0.087	0.039	0.010	0.010
26	0.086	2.11	0.279	0.405	1.87	1.04	0.404	0.219	0.087	0.039	0.010	0.010
27	0.086	0.909	0.253	0.405	1.97	0.973	0.404	0.219	0.087	0.039	0.010	0.010
28	0.086	0.506	0.253	0.355	1.56	0.905	0.404	0.219	0.064	0.039	0.010	0.010
29	0.086	0.355	0.279	0.355	-----	0.905	0.404	0.219	0.064	0.039	0.010	0.010
30	0.106	0.304	0.304	0.355	-----	0.905	0.404	0.219	0.064	0.039	0.010	0.010
31	0.125	-----	0.694	0.355	-----	0.838	-----	0.219	-----	0.039	0.010	-----
Maks.	0.125	4.07	3.58	1.50	14.3	23.9	1.35	0.404	0.219	0.051	0.039	0.010
Min.	0.056	0.125	0.253	0.279	0.355	0.838	0.404	0.219	0.064	0.039	0.010	0.010
Ortalama	0.076	0.322	0.366	0.382	1.61	2.07	0.534	0.291	0.128	0.048	0.017	0.010
LT/SN/Km2	1.09	4.65	5.30	5.53	23.3	30.0	7.73	4.21	1.86	0.699	0.239	0.145
AKIM mm.	2.93	12.1	14.2	14.8	56.4	80.2	20.0	11.3	4.81	1.87	0.641	0.375
MİL. M3	0.203	0.834	0.981	1.02	3.90	5.54	1.38	0.778	0.333	0.129	0.044	0.026

SU YILI (2006) YILLIK TOPLAM AKIM 15.17 MİLYON M3 220 MM. 7.0 LT/SN/Km2

06. Küçük Menderes Havzasi

D06A026 PİRİNÇCI Ç. BADEMLİ

YERİ : **ÖDEMİŞ ADAGİDE PİRİNÇCİ KÖY YOLUNUN 5.5 KM.SİNDEKİ BADEMLİ BELDESİNDEDİR.(PAFTA L20-D4)**
28°4'0" Doğu - 38°5'19" Kuzey

YAĞIŞ ALANI : **38,40 km2** **YAKLAŞIK KOT : 250 m**

GÖZLEM SÜRESİ : **01.10.1996 - 30.09.2006**

ORTALAMA AKIMLAR : **Gözlem süresinde 0.584 m3/sn. (6 Yıllık) 2006 Su yılında 0.974 m3/sn.**

ANLIK EN ÇOK VE EN AZ AKIMLAR:

2006 Su yılında anlık ençok akım	**:**	**15.1**	**m3/sn**	**19.01.2006**
2006 Su yılında anlık enaz akım	**:**	**0.000**	**m3/sn**	**01.10.2005**
Gözlem süresinde anlık ençok akım	**:**	**26.9**	**m3/sn**	**24.11.2001**
Gözlem süresinde anlık enaz akım	**:**	**0.000**	**m3/sn**	**01.10.1999**

4. Anahtar Eğrisi (Seviyeler cm olarak)

Seviye	Akım	Seviye	Akım	Seviye	Akım	Seviye	Akım
1	0.000	20	0.033	47	2.0	150	22.2
4	0.000	25	0.138	60	4.2	160	24.5
7	0.000	30	0.346	90	9.3	170	26.8
10	0.000	35	0.724	120	15.3	190	33.1
17	0.012	40	1.2	130	17.6		

Akımlar 01 Ekim 2005 'den 30 Eylül 2006' a kadar m3/sn olarak

Gün	Ekim	Kasım	Aralık	Ocak	Şubat	Mart	Nisan	Mayıs	Haziran	Temmuz	Ağustos	Eylül
01	KURU	KURU	0.474	0.891	2.34	2.16	2.16	0.811	0.550	0.033	KURU	KURU
02	KURU	KURU	0.398	0.811	2.53	1.86	2.16	0.811	0.398	0.033	KURU	KURU
03	KURU	KURU	0.398	0.724	2.34	1.97	1.75	0.811	0.398	0.033	KURU	KURU
04	KURU	KURU	0.346	0.724	2.53	1.75	1.64	0.811	0.398	0.033	KURU	KURU
05	KURU	KURU	0.346	0.891	2.53	1.64	1.64	0.811	0.398	0.021	KURU	KURU
06	KURU	KURU	0.294	0.891	4.35	1.54	1.64	0.724	0.398	0.021	KURU	KURU
07	KURU	KURU	0.294	0.970	3.83	2.34	1.64	0.724	0.346	0.021	KURU	KURU
08	KURU	KURU	0.241	0.970	4.01	4.51	1.64	0.724	0.346	0.021	KURU	KURU
09	KURU	KURU	0.241	0.891	4.01	3.48	1.54	0.637	0.346	0.021	KURU	KURU
10	KURU	KURU	0.241	0.811	5.67	3.00	1.54	0.637	0.346	0.017	KURU	KURU
11	KURU	KURU	0.241	0.724	8.58	2.69	1.43	0.637	0.346	0.005	KURU	KURU
12	KURU	0.003	0.205	0.724	6.17	3.31	1.18	0.637	0.205	0.003	KURU	KURU
13	KURU	0.005	0.205	0.637	4.84	5.50	1.18	0.637	0.205	KURU	KURU	KURU
14	KURU	0.033	0.205	0.550	4.01	6.84	1.18	0.637	0.138	KURU	KURU	KURU
15	KURU	0.033	0.294	0.550	3.31	5.83	1.18	0.637	0.138	KURU	KURU	KURU
16	KURU	0.033	0.241	0.474	3.31	5.34	1.31	0.637	0.138	KURU	KURU	KURU
17	KURU	0.045	0.241	0.474	3.31	4.68	1.31	0.550	0.075	KURU	KURU	KURU
18	KURU	0.637	0.474	0.474	3.48	4.35	1.31	0.550	0.075	KURU	KURU	KURU
19	KURU	0.169	1.43	5.17	3.48	4.01	1.31	0.550	0.075	KURU	KURU	KURU
20	KURU	0.346	0.724	4.35	3.48	3.83	1.31	0.550	0.075	KURU	KURU	KURU
21	KURU	0.060	0.550	4.18	3.48	3.83	1.05	0.550	0.045	KURU	KURU	KURU
22	KURU	0.033	0.474	4.01	3.48	3.83	1.05	0.346	0.045	KURU	KURU	KURU
23	KURU	0.169	0.398	3.48	3.48	3.83	1.05	0.346	0.045	KURU	KURU	KURU
24	KURU	0.637	0.398	2.84	3.48	3.66	1.05	0.294	0.045	KURU	KURU	KURU
25	KURU	1.05	0.346	2.69	3.48	3.48	0.970	0.294	0.045	KURU	KURU	KURU
26	KURU	5.34	0.346	2.69	3.48	3.31	0.970	0.294	0.033	KURU	KURU	KURU
27	KURU	1.86	0.346	2.53	3.00	3.31	0.811	0.294	0.033	KURU	KURU	KURU
28	KURU	0.970	0.346	2.53	1.97	3.31	0.811	0.294	0.033	KURU	KURU	KURU
29	KURU	0.811	1.05	2.53	-----	3.00	0.811	0.474	0.033	KURU	KURU	KURU
30	KURU	0.637	0.637	2.53	-----	2.34	0.891	0.474	0.033	KURU	KURU	KURU
31	KURU	-----	0.970	2.53	-----	2.34	-----	0.474	-----	KURU	KURU	-----
Maks.	KURU	9.47	3.48	15.1	11.9	8.40	2.16	0.811	0.550	0.033	KURU	KURU
Min.	KURU	KURU	0.205	0.474	1.97	1.54	0.811	0.294	KURU	KURU	KURU	KURU
Ortalama	KURU	0.429	0.432	1.78	3.71	3.45	1.32	0.570	0.193	0.008	KURU	KURU
LT/SN/Km2	0.000	11.2	11.3	46.4	96.7	89.8	34.3	14.8	5.02	0.220	0.000	0.000
AKIM mm.	0.000	29.0	30.1	124.	234.	240.	88.9	39.7	13.0	0.589	0.000	0.000
MİL. M3	0.000	1.11	1.16	4.77	8.98	9.23	3.41	1.53	0.500	0.023	0.000	0.000

SU YILI (2006) YILLIK TOPLAM AKIM 30.71 MİLYON M3 800 MM. 25.4 LT/SN/Km2

06. Küçük Menderes Havzasi

D06A027 ILICA D. ERGENLİ

YERİ : **BAYINDIR İLÇESİ ERGENLİ KÖYÜ ILICA TESİSLERİNDEDİR. (PAFTA L19-A3)**
27°41'12" Doğu - 38°15'4" Kuzey

YAĞIŞ ALANI : **57,00 km2** **YAKLAŞIK KOT : 14 m**

GÖZLEM SÜRESİ : **01.10.1996 - 30.09.2006**

ORTALAMA AKIMLAR : **Gözlem süresinde 0.318 m3/sn. (6 Yıllık) 2006 Su yılında 0.423 m3/sn.**

ANLIK EN ÇOK VE EN AZ AKIMLAR:

2006 Su yılında anlık ençok akım	:	**13.1**	**m3/sn**	**11.02.2006**
2006 Su yılında anlık enaz akım	:	**0.005**	**m3/sn**	**01.10.2005**
Gözlem süresinde anlık ençok akım	:	**26.3**	**m3/sn**	**07.02.2003**
Gözlem süresinde anlık enaz akım	:	**0.000**	**m3/sn**	**24.06.2004**

3. Anahtar Eğrisi (Seviyeler cm olarak)

Seviye	Akım	Seviye	Akım	Seviye	Akım	Seviye	Akım
1	0.000	16	0.000	34	0.125	130	18.3
4	0.000	19	0.000	42	0.626	140	20.8
7	0.000	22	0.000	60	2.7	150	23.3
10	0.000	25	0.000	90	8.4	160	25.8
13	0.000	28	0.000	120	15.8	165	27.0

Akımlar 01 Ekim 2005 'den 30 Eylül 2006' a kadar m3/sn olarak

Gün	Ekim	Kasım	Aralık	Ocak	Şubat	Mart	Nisan	Mayıs	Haziran	Temmuz	Ağustos	Eylül
01	0.005	0.005	0.366	0.626	0.366	1.28	0.517	0.128	0.076	0.005	0.005	0.005
02	0.005	0.005	0.366	0.517	0.325	1.28	1.28	0.161	0.076	0.005	0.005	0.005
03	0.005	0.005	0.366	0.408	0.366	1.28	2.03	0.161	0.042	0.005	0.005	0.005
04	0.005	0.005	0.366	0.325	0.366	1.28	0.722	0.161	0.042	0.005	0.005	0.005
05	0.005	0.005	0.366	0.325	0.366	1.28	0.819	0.242	0.042	0.005	0.005	0.005
06	0.005	0.005	0.366	0.283	0.366	1.28	0.819	0.242	0.042	0.005	0.005	0.005
07	0.005	0.005	0.366	0.283	1.01	1.28	0.722	0.242	0.042	0.005	0.005	0.005
08	0.005	0.019	0.366	0.325	1.50	3.21	0.572	0.202	0.042	0.005	0.005	0.005
09	0.005	0.042	0.366	0.325	1.19	2.29	0.572	0.202	0.042	0.005	0.005	0.005
10	0.005	0.042	0.366	0.283	1.10	1.76	0.572	0.283	0.042	0.005	0.005	0.005
11	0.005	0.042	0.366	0.283	2.82	1.63	0.572	0.283	0.042	0.005	0.005	0.005
12	0.005	0.042	0.366	0.283	7.17	4.40	0.572	0.283	0.042	0.005	0.005	0.005
13	0.005	0.042	0.366	0.283	3.61	4.20	0.572	0.408	0.042	0.005	0.005	0.005
14	0.005	0.042	0.283	0.283	2.16	4.20	0.572	0.202	0.042	0.005	0.005	0.005
15	0.005	0.042	0.242	0.283	1.76	3.47	0.517	0.242	0.042	0.005	0.005	0.005
16	0.005	0.042	0.242	0.283	1.50	3.47	0.463	0.202	0.012	0.005	0.005	0.005
17	0.005	0.057	0.242	0.283	1.50	3.34	0.408	0.202	0.005	0.005	0.005	0.005
18	0.005	0.408	0.325	0.283	1.37	2.42	0.366	0.161	0.005	0.005	0.005	0.005
19	0.005	0.283	2.29	1.19	1.19	2.03	0.366	0.161	0.005	0.005	0.005	0.005
20	0.005	0.283	1.01	2.82	0.915	1.37	0.325	0.161	0.005	0.005	0.005	0.005
21	0.005	0.242	0.463	1.01	0.626	1.28	0.242	0.161	0.005	0.005	0.005	0.005
22	0.005	0.128	0.366	0.626	0.626	1.28	0.242	0.161	0.005	0.005	0.005	0.005
23	0.005	0.076	0.366	0.626	0.517	1.19	0.242	0.161	0.005	0.005	0.005	0.005
24	0.005	0.128	0.366	0.626	0.915	1.19	0.202	0.161	0.005	0.005	0.005	0.005
25	0.005	0.202	0.366	0.819	1.10	1.01	0.202	0.161	0.005	0.005	0.005	0.005
26	0.005	2.42	0.366	0.915	1.28	0.819	0.161	0.161	0.005	0.005	0.005	0.005
27	0.005	0.722	0.366	0.626	1.28	0.819	0.161	0.161	0.005	0.005	0.005	0.005
28	0.005	0.463	0.366	0.408	1.28	0.626	0.128	0.161	0.005	0.005	0.005	0.005
29	0.005	0.366	0.366	0.366	-----	0.626	0.128	0.094	0.005	0.005	0.005	0.005
30	0.005	0.366	0.283	0.366	-----	0.572	0.128	0.076	0.005	0.005	0.005	0.005
31	0.005	-----	0.463	0.366	-----	0.517	-----	0.076	-----	0.005	0.005	-----
Maks.	0.005	3.34	4.99	7.65	13.1	5.58	4.00	0.517	0.076	0.005	0.005	0.005
Min.	0.005	0.005	0.161	0.283	0.325	0.517	0.128	0.026	0.005	0.005	0.005	0.005
Ortalama	0.005	0.218	0.436	0.540	1.38	1.83	0.506	0.189	0.026	0.005	0.005	0.005
LT/SN/Km2	0.088	3.82	7.66	9.47	24.2	32.1	8.89	3.32	0.456	0.088	0.088	0.088
AKIM mm.	0.235	9.90	20.5	25.4	58.5	85.9	23.0	8.89	1.18	0.235	0.235	0.227
MİL. M3	0.013	0.565	1.17	1.45	3.33	4.90	1.31	0.507	0.067	0.013	0.013	0.013

SU YILI (2006) YILLIK TOPLAM AKIM 13.35 MİLYON M3 234 MM. 7.4 LT/SN/Km2

06. Küçük Menderes Havzasi

D06A028 DERİNCE D. KÜÇÜKBAHÇE

YERİ : **BALIKLIOVA KÜÇÜKBAHÇE KARAYOLU KÖPRÜSÜNÜN 40 M MEMBAĞINDADIR. (PAFTA K16-C3)**
26°22'29" Doğu - 38°34'18" Kuzey

YAĞIŞ ALANI : **30,25 km2** **YAKLAŞIK KOT : 8 m**

GÖZLEM SÜRESİ : **01.10.1996 - 30.09.2006**

ORTALAMA AKIMLAR : **Gözlem süresinde 0.180 m3/sn. (3 Yıllık) 2006 Su yılında 0.075 m3/sn.**

ANLIK EN ÇOK VE EN AZ AKIMLAR:

2006 Su yılında anlık ençok akım	:	**4.94**	**m3/sn**	**08.02.2006**
2006 Su yılında anlık enaz akım	:	**0.000**	**m3/sn**	**01.10.2005**
Gözlem süresinde anlık ençok akım	:	**19.9**	**m3/sn**	**16.02.2005**
Gözlem süresinde anlık enaz akım	:	**0.000**	**m3/sn**	**01.10.2002**

İstasyon için kullanılmış anahtar bulunamadı.

Akımlar 01 Ekim 2005 'den 30 Eylül 2006' a kadar m3/sn olarak

Gün	Ekim	Kasım	Aralık	Ocak	Şubat	Mart	Nisan	Mayıs	Haziran	Temmuz	Ağustos	Eylül
01	KURU	KURU	0.035	0.035	0.027	0.035	0.032	KURU	KURU	KURU	KURU	KURU
02	KURU	KURU	0.032	0.035	0.030	0.035	0.032	KURU	KURU	KURU	KURU	KURU
03	KURU	KURU	0.035	0.035	0.023	0.035	0.032	KURU	KURU	KURU	KURU	KURU
04	KURU	KURU	0.035	0.035	0.018	0.035	0.032	KURU	KURU	KURU	KURU	KURU
05	KURU	KURU	0.035	0.035	0.016	0.035	0.032	KURU	KURU	KURU	KURU	KURU
06	KURU	KURU	0.035	0.035	0.027	0.035	0.032	KURU	KURU	KURU	KURU	KURU
07	KURU	KURU	0.035	0.035	0.078	0.051	0.032	KURU	KURU	KURU	KURU	KURU
08	KURU	KURU	0.035	0.035	2.57	1.42	0.032	KURU	KURU	KURU	KURU	KURU
09	KURU	KURU	0.035	0.035	1.42	0.557	0.032	KURU	KURU	KURU	KURU	KURU
10	KURU	KURU	0.035	0.035	1.54	0.078	0.032	KURU	KURU	KURU	KURU	KURU
11	KURU	KURU	0.035	0.035	1.03	0.072	0.032	KURU	KURU	KURU	KURU	KURU
12	KURU	KURU	0.035	0.035	0.715	0.399	0.032	KURU	KURU	KURU	KURU	KURU
13	KURU	KURU	0.035	0.035	0.399	3.62	0.032	KURU	KURU	KURU	KURU	KURU
14	KURU	KURU	0.035	0.035	0.242	2.06	0.032	KURU	KURU	KURU	KURU	KURU
15	KURU	KURU	0.035	0.035	0.078	1.16	0.032	KURU	KURU	KURU	KURU	KURU
16	KURU	KURU	0.035	0.035	0.072	1.03	0.032	KURU	KURU	KURU	KURU	KURU
17	KURU	KURU	0.035	0.035	0.060	0.715	0.032	KURU	KURU	KURU	KURU	KURU
18	KURU	KURU	0.035	0.035	0.054	1.42	0.032	KURU	KURU	KURU	KURU	KURU
19	KURU	KURU	0.035	0.035	0.051	1.16	0.032	KURU	KURU	KURU	KURU	KURU
20	KURU	KURU	0.035	0.035	0.040	0.715	0.032	KURU	KURU	KURU	KURU	KURU
21	KURU	KURU	0.035	0.035	0.035	0.399	0.032	KURU	KURU	KURU	KURU	KURU
22	KURU	KURU	0.035	0.035	0.035	0.084	0.032	KURU	KURU	KURU	KURU	KURU
23	KURU	KURU	0.035	0.066	0.035	0.072	0.032	KURU	KURU	KURU	KURU	KURU
24	KURU	0.037	0.035	KURU	0.035	0.066	0.032	KURU	KURU	KURU	KURU	KURU
25	KURU	0.021	0.035	0.030	0.035	0.066	0.032	KURU	KURU	KURU	KURU	KURU
26	KURU	0.018	0.035	0.023	0.035	0.051	0.032	KURU	KURU	KURU	KURU	KURU
27	KURU	0.030	0.035	0.021	0.035	0.047	KURU	KURU	KURU	KURU	KURU	KURU
28	KURU	0.032	0.035	0.021	0.035	0.035	KURU	KURU	KURU	KURU	KURU	KURU
29	KURU	0.060	0.035	0.023	-----	0.032	KURU	KURU	KURU	KURU	KURU	KURU
30	KURU	0.047	0.035	0.027	-----	0.032	KURU	KURU	KURU	KURU	KURU	KURU
31	KURU	-----	0.035	0.032	-----	0.032	-----	KURU	-----	KURU	KURU	-----
Maks.	KURU	0.060	0.035	0.066	4.94	3.62	0.032	KURU	KURU	KURU	KURU	KURU
Min.	KURU	KURU	0.032	KURU	0.016	0.032	KURU	KURU	KURU	KURU	KURU	KURU
Ortalama	KURU	0.008	0.035	0.033	0.313	0.503	0.028	KURU	KURU	KURU	KURU	KURU
LT/SN/Km2	0.000	0.270	1.15	1.08	10.4	16.6	0.917	0.000	0.000	0.000	0.000	0.000
AKIM mm.	0.000	0.700	3.09	2.89	25.0	44.5	2.38	0.000	0.000	0.000	0.000	0.000
MİL. M3	0.000	0.021	0.093	0.088	0.758	1.35	0.072	0.000	0.000	0.000	0.000	0.000

SU YILI (2006) YILLIK TOPLAM AKIM 2.38 MİLYON M3 79 MM. 2.5 LT/SN/Km2

06. Küçük Menderes Havzasi

D06A029 CAMİBOGAZI D. KARAREİS ÇIFTL.

YERİ : **BALIKLIOVA-KÜÇÜKBAHÇE KARAYOLUNUN 22 . KM SİNDEN SOLA DÖNEN YOLUN 400 M.SİNDEDİR (PAFTA L16-B2) 26°25'40" Doğu - 38°28'0" Kuzey**

YAĞIŞ ALANI : **59,20 km2** **YAKLAŞIK KOT : 5 m**

GÖZLEM SÜRESİ : **01.10.1996 - 30.09.2006**

ORTALAMA AKIMLAR : **Gözlem süresinde 0.171 m3/sn. (5 Yıllık) 2006 Su yılında 0.059 m3/sn.**

ANLIK EN ÇOK VE EN AZ AKIMLAR:

2006 Su yılında anlık ençok akım	**:**	**11.7**	**m3/sn**	**13.03.2006**
2006 Su yılında anlık enaz akım	**:**	**0.000**	**m3/sn**	**01.10.2005**
Gözlem süresinde anlık ençok akım	**:**	**20.4**	**m3/sn**	**22.01.2004**
Gözlem süresinde anlık enaz akım	**:**	**0.000**	**m3/sn**	**01.10.2001**

İstasyon için kullanılmış anahtar bulunamadı.

Akımlar 01 Ekim 2005 'den 30 Eylül 2006' a kadar m3/sn olarak

Gün	Ekim	Kasım	Aralık	Ocak	Şubat	Mart	Nisan	Mayıs	Haziran	Temmuz	Ağustos	Eylül
01	KURU	KURU	0.079	0.007	0.014	0.125	0.140	0.020	KURU	KURU	KURU	KURU
02	KURU	KURU	0.079	0.007	0.063	0.125	0.140	0.014	KURU	KURU	KURU	KURU
03	KURU	KURU	0.079	0.007	0.184	0.125	0.140	0.014	KURU	KURU	KURU	KURU
04	KURU	KURU	0.079	0.007	0.090	0.125	0.140	0.007	KURU	KURU	KURU	KURU
05	KURU	KURU	0.079	0.007	0.090	0.125	0.125	0.007	KURU	KURU	KURU	KURU
06	KURU	KURU	0.079	0.007	0.544	0.125	0.125	0.004	KURU	KURU	KURU	KURU
07	KURU	KURU	0.079	0.007	0.184	0.232	0.125	0.004	KURU	KURU	KURU	KURU
08	KURU	KURU	0.079	0.007	0.159	0.591	0.125	KURU	KURU	KURU	KURU	KURU
09	KURU	KURU	0.079	0.007	0.184	0.171	0.125	KURU	KURU	KURU	KURU	KURU
10	KURU	KURU	0.079	0.007	0.731	0.140	0.125	KURU	KURU	KURU	KURU	KURU
11	KURU	KURU	0.079	0.007	0.262	0.063	0.125	KURU	KURU	KURU	KURU	KURU
12	KURU	KURU	0.079	0.007	0.140	0.027	0.125	KURU	KURU	KURU	KURU	KURU
13	KURU	KURU	0.079	0.007	0.109	2.49	0.125	KURU	KURU	KURU	KURU	KURU
14	KURU	KURU	0.079	0.007	0.125	1.57	0.125	KURU	KURU	KURU	KURU	KURU
15	KURU	KURU	0.079	0.007	0.125	0.684	0.125	KURU	KURU	KURU	KURU	KURU
16	KURU	KURU	0.079	0.007	0.125	0.457	0.125	KURU	KURU	KURU	KURU	KURU
17	KURU	KURU	0.079	0.007	0.125	0.293	0.125	KURU	KURU	KURU	KURU	KURU
18	KURU	KURU	0.079	0.007	0.125	0.962	0.125	KURU	KURU	KURU	KURU	KURU
19	KURU	KURU	0.014	0.007	0.125	0.684	0.125	KURU	KURU	KURU	KURU	KURU
20	KURU	KURU	0.007	0.007	0.125	0.375	0.125	KURU	KURU	KURU	KURU	KURU
21	KURU	KURU	0.007	0.007	0.125	0.232	0.125	KURU	KURU	KURU	KURU	KURU
22	KURU	KURU	0.007	0.007	0.125	0.171	0.125	KURU	KURU	KURU	KURU	KURU
23	KURU	KURU	0.007	0.007	0.125	0.171	0.125	KURU	KURU	KURU	KURU	KURU
24	KURU	KURU	0.007	0.010	0.125	0.201	0.125	KURU	KURU	KURU	KURU	KURU
25	KURU	0.002	0.007	0.010	0.125	0.201	0.125	KURU	KURU	KURU	KURU	KURU
26	KURU	0.004	0.007	0.010	0.125	0.171	0.125	KURU	KURU	KURU	KURU	KURU
27	KURU	0.014	0.007	0.010	0.125	0.171	0.125	KURU	KURU	KURU	KURU	KURU
28	KURU	0.034	0.007	0.010	0.125	0.140	0.041	KURU	KURU	KURU	KURU	KURU
29	KURU	0.063	0.007	0.010	-----	0.140	0.020	KURU	KURU	KURU	KURU	KURU
30	KURU	0.063	0.007	0.010	-----	0.140	0.020	KURU	KURU	KURU	KURU	KURU
31	KURU	-----	0.007	0.014	-----	0.140	-----	KURU	-----	KURU	KURU	-----
Maks.	KURU	0.109	0.416	0.014	1.65	11.7	0.140	0.020	KURU	KURU	KURU	KURU
Min.	KURU	KURU	0.007	0.007	0.010	0.027	0.014	KURU	KURU	KURU	KURU	KURU
Ortalama	KURU	0.006	0.049	0.008	0.165	0.367	0.117	0.002	KURU	KURU	KURU	KURU
LT/SN/Km2	0.000	0.101	0.828	0.134	2.79	6.19	1.98	0.038	0.000	0.000	0.000	0.000
AKIM mm.	0.000	0.263	2.22	0.358	6.76	16.6	5.13	0.102	0.000	0.000	0.000	0.000
MİL. M3	0.000	0.016	0.131	0.021	0.400	0.982	0.304	0.006	0.000	0.000	0.000	0.000

SU YILI (2006) YILLIK TOPLAM AKIM 1.86 MİLYON M3 31 MM. 1.0 LT/SN/Km2

06. Küçük Menderes Havzasi

D06A033 KİRAZ Ç. KİRAZ

YERİ : **KİRAZ-HİSAR KÖYÜNÜN ÇIKIŞINDAKİ KÖPRÜNÜN 20 M MENBAĞINDADIR.(PAFTA L20-D2)**
29°11'9" Doğu - 38°13'49" Kuzey

YAĞIŞ ALANI : **114,40 km2** **YAKLAŞIK KOT : 351 m**

GÖZLEM SÜRESİ : **01.01.2005 - 30.09.2006**

ORTALAMA AKIMLAR : **Gözlem süresinde 1.375 m3/sn. (1 Yıllık) 2006 Su yılında 1.375 m3/sn.**

ANLIK EN ÇOK VE EN AZ AKIMLAR:

2006 Su yılında anlık ençok akım	:	**22.8**	**m3/sn**	**11.02.2006**
2006 Su yılında anlık enaz akım	:	**0.000**	**m3/sn**	**01.10.2005**
Gözlem süresinde anlık ençok akım	:	**22.8**	**m3/sn**	**11.02.2006**
Gözlem süresinde anlık enaz akım	:	**0.000**	**m3/sn**	**01.10.2005**

4. Anahtar Eğrisi (Seviyeler cm olarak)

Seviye	Akım	Seviye	Akım	Seviye	Akım
30	0.000	55	1.0	100	9.2
40	0.000	60	1.5	110	11.4
41	0.001	70	3.0	120	13.7
46	0.048	80	5.0	130	16.2
50	0.250	90	7.1	140	18.8

Akımlar 01 Ekim 2005 'den 30 Eylül 2006' a kadar m3/sn olarak

Gün	Ekim	Kasım	Aralık	Ocak	Şubat	Mart	Nisan	Mayıs	Haziran	Temmuz	Ağustos	Eylül
01	KURU	KURU	1.28	1.87	1.47	3.51	3.51	8.76	0.405	KURU	KURU	KURU
02	KURU	KURU	1.08	1.67	1.47	3.22	3.22	0.886	0.405	KURU	KURU	KURU
03	KURU	KURU	1.08	1.47	1.47	3.51	3.22	1.87	0.310	KURU	KURU	KURU
04	KURU	KURU	0.886	1.47	1.28	3.51	3.51	1.67	0.215	KURU	KURU	KURU
05	KURU	KURU	0.886	1.67	1.28	3.22	3.22	1.87	0.215	KURU	KURU	KURU
06	KURU	KURU	0.690	1.67	2.45	3.22	3.22	1.67	0.120	KURU	KURU	KURU
07	KURU	KURU	0.690	1.67	3.22	3.51	2.94	1.87	0.215	KURU	KURU	KURU
08	KURU	KURU	0.690	1.47	2.94	3.51	2.94	1.08	0.062	KURU	KURU	KURU
09	KURU	KURU	0.690	1.47	2.45	4.65	2.94	1.28	0.405	KURU	KURU	KURU
10	KURU	KURU	0.595	1.28	4.08	3.79	2.65	4.65	0.405	KURU	KURU	KURU
11	KURU	KURU	0.595	1.28	13.6	3.22	2.65	2.45	0.405	KURU	KURU	KURU
12	KURU	KURU	0.595	1.28	8.40	3.22	2.65	0.595	0.405	KURU	KURU	KURU
13	KURU	KURU	0.595	1.08	5.79	5.79	2.65	0.690	0.310	KURU	KURU	KURU
14	KURU	KURU	0.595	1.08	4.65	10.2	2.94	1.47	0.405	KURU	KURU	KURU
15	KURU	KURU	0.595	1.08	3.79	4.93	2.65	1.28	0.310	KURU	KURU	KURU
16	KURU	KURU	0.690	1.08	3.22	4.36	2.45	1.28	0.310	KURU	KURU	KURU
17	KURU	KURU	0.690	1.08	3.22	3.51	2.26	1.08	0.042	KURU	KURU	KURU
18	KURU	0.215	1.08	0.886	3.22	3.51	2.26	1.08	0.042	KURU	KURU	KURU
19	KURU	0.081	3.22	2.65	3.22	3.51	2.06	0.886	KURU	KURU	KURU	KURU
20	KURU	0.101	1.87	3.22	2.94	3.51	2.06	0.886	KURU	KURU	KURU	KURU
21	KURU	0.120	1.47	2.06	2.94	3.51	2.06	0.886	KURU	KURU	KURU	KURU
22	KURU	0.500	1.28	2.06	2.65	3.51	2.06	0.886	KURU	KURU	KURU	KURU
23	KURU	0.405	1.28	1.87	2.65	3.79	2.06	0.690	KURU	KURU	KURU	KURU
24	KURU	0.595	1.08	2.06	2.65	4.08	5.22	0.690	KURU	KURU	KURU	KURU
25	KURU	1.87	1.08	2.45	3.79	4.08	8.76	0.690	KURU	KURU	KURU	KURU
26	KURU	6.66	1.08	2.06	4.36	3.79	8.40	0.595	KURU	KURU	KURU	KURU
27	KURU	3.79	0.886	1.87	3.79	3.79	8.40	0.595	KURU	KURU	KURU	KURU
28	KURU	2.26	0.886	1.67	3.51	3.51	8.40	0.595	KURU	KURU	KURU	KURU
29	KURU	1.67	1.08	1.67	-----	3.51	10.9	0.500	KURU	KURU	KURU	KURU
30	KURU	1.47	1.08	1.47	-----	3.51	14.8	0.500	KURU	KURU	KURU	KURU
31	KURU	-----	1.67	1.47	-----	3.51	-----	0.500	-----	KURU	KURU	-----
Maks.	KURU	9.48	5.50	8.40	22.8	21.2	18.0	18.0	0.405	KURU	KURU	KURU
Min.	KURU	KURU	0.595	0.886	1.28	3.22	1.87	0.405	KURU	KURU	KURU	KURU
Ortalama	KURU	0.658	1.03	1.65	3.59	3.94	4.24	1.43	0.166	KURU	KURU	KURU
LT/SN/Km2	0.000	5.75	9.01	14.4	31.4	34.4	37.0	12.5	1.45	0.000	0.000	0.000
AKIM mm.	0.000	14.9	24.1	38.6	75.9	92.1	96.0	33.6	3.77	0.000	0.000	0.000
MİL. M3	0.000	1.71	2.76	4.42	8.68	10.5	11.0	3.84	0.431	0.000	0.000	0.000

SU YILI (2006) YILLIK TOPLAM AKIM 43.34 MİLYON M3 379 MM. 12.0 LT/SN/Km2

06. Küçük Menderes Havzasi

D06A034 KIZILKAYA D. YENİSEHİR

YERİ : **TİRE-GÖKÇEN KASABASINDAN SONRA SAĞA AYRILAN YOLUN 7. KM SİNDEDİR.(PAFTA D19-C4)**
27°54'33" Doğu - 38°3'27" Kuzey

YAĞIŞ ALANI : **15,40 km2** **YAKLAŞIK KOT : 312 m**

GÖZLEM SÜRESİ : **01.01.2005 - 30.09.2006**

ORTALAMA AKIMLAR : **Gözlem süresinde 0.201 m3/sn. (1 Yıllık) 2006 Su yılında 0.201 m3/sn.**

ANLIK EN ÇOK VE EN AZ AKIMLAR:

2006 Su yılında anlık ençok akım	:	**5.28**	**m3/sn**	**25.11.2005**
2006 Su yılında anlık enaz akım	:	**0.000**	**m3/sn**	**01.10.2005**
Gözlem süresinde anlık ençok akım	:	**5.28**	**m3/sn**	**25.11.2005**
Gözlem süresinde anlık enaz akım	:	**0.000**	**m3/sn**	**01.10.2005**

6. Anahtar Eğrisi (Seviyeler cm olarak)

Seviye	Akım	Seviye	Akım	Seviye	Akım	Seviye	Akım
20	0.000	36	0.006	48	0.180	80	3.8
31	0.000	38	0.013	50	0.320	90	5.4
33	0.002	40	0.025	55	0.690	100	7.0
34	0.003	42	0.045	60	1.2	150	17.0
35	0.004	46	0.127	70	2.4	167	21.0

Akımlar 01 Ekim 2005 'den 30 Eylül 2006' a kadar m3/sn olarak

Gün	Ekim	Kasım	Aralık	Ocak	Şubat	Mart	Nisan	Mayıs	Haziran	Temmuz	Ağustos	Eylül
01	KURU	0.001	0.024	0.037	0.070	0.396	0.927	0.312	0.071	KURU	KURU	KURU
02	KURU	0.002	0.070	0.031	0.081	0.396	0.927	0.150	0.071	KURU	KURU	KURU
03	KURU	0.002	0.070	0.031	1.81	0.312	0.927	0.231	0.071	KURU	KURU	KURU
04	KURU	0.002	0.031	0.031	1.65	0.312	0.927	0.150	0.071	KURU	KURU	KURU
05	KURU	0.002	0.031	0.031	1.48	0.312	0.927	0.098	0.071	KURU	KURU	KURU
06	0.002	0.002	0.031	0.037	0.480	0.312	0.833	0.098	0.071	KURU	KURU	KURU
07	KURU	0.004	0.031	0.037	0.396	0.312	0.833	0.098	0.071	KURU	KURU	KURU
08	0.004	0.006	0.031	0.031	0.231	0.833	0.833	0.124	0.071	KURU	KURU	KURU
09	0.001	0.002	0.031	0.037	0.150	1.02	0.833	0.098	0.071	KURU	KURU	KURU
10	KURU	0.001	0.031	0.037	0.396	1.11	0.833	0.098	0.071	KURU	KURU	KURU
11	KURU	KURU	0.031	0.037	1.02	1.02	0.833	0.071	0.071	KURU	KURU	KURU
12	KURU	KURU	0.031	0.031	0.740	0.927	0.833	0.071	0.045	KURU	KURU	KURU
13	KURU	KURU	0.031	0.031	0.740	1.30	0.833	0.071	0.045	KURU	KURU	KURU
14	KURU	KURU	0.031	0.031	0.740	1.65	0.833	0.071	0.045	KURU	KURU	KURU
15	KURU	KURU	0.059	0.031	0.833	1.48	0.740	0.071	0.045	KURU	KURU	KURU
16	0.006	KURU	0.037	0.031	0.833	1.30	0.740	0.071	0.045	KURU	KURU	KURU
17	0.002	0.003	0.037	0.031	0.740	1.11	0.740	0.071	0.045	KURU	KURU	KURU
18	0.002	0.035	0.059	0.031	0.740	1.11	0.740	0.045	0.025	KURU	KURU	KURU
19	0.002	0.045	0.037	0.070	0.610	1.02	0.610	0.045	0.025	KURU	KURU	KURU
20	0.002	0.071	0.037	0.081	0.610	0.833	0.610	0.045	0.025	KURU	KURU	KURU
21	0.002	0.045	0.037	0.081	0.480	0.740	0.610	0.045	0.013	KURU	KURU	KURU
22	0.002	0.045	0.031	0.070	0.396	0.740	0.610	0.045	0.013	KURU	KURU	KURU
23	0.002	0.071	0.031	0.070	0.396	0.740	0.480	0.045	0.006	KURU	KURU	KURU
24	0.001	0.045	0.031	0.070	0.396	0.927	0.480	0.045	0.006	KURU	KURU	KURU
25	0.001	0.045	0.031	0.081	0.312	1.21	0.480	0.045	0.003	KURU	KURU	KURU
26	0.001	0.081	0.031	0.081	0.312	1.02	0.480	0.045	0.004	KURU	KURU	KURU
27	0.001	0.037	0.031	0.081	0.312	1.02	0.480	0.071	0.002	KURU	KURU	KURU
28	0.001	0.031	0.031	0.081	0.312	1.02	0.480	0.071	0.001	KURU	KURU	KURU
29	0.001	0.024	0.031	0.081	-----	1.02	0.396	0.071	KURU	KURU	KURU	KURU
30	0.001	0.031	0.031	0.070	-----	1.02	0.396	0.071	KURU	KURU	KURU	KURU
31	0.001	-----	0.031	0.070	-----	1.02	-----	0.071	-----	KURU	KURU	-----
Maks.	0.013	5.28	0.548	0.081	1.81	2.58	1.11	2.58	0.071	KURU	KURU	KURU
Min.	KURU	KURU	0.024	0.031	0.070	0.312	0.396	0.045	KURU	KURU	KURU	KURU
Ortalama	0.001	0.021	0.036	0.051	0.617	0.888	0.707	0.088	0.039	KURU	KURU	KURU
LT/SN/Km2	0.073	1.37	2.34	3.31	40.0	57.7	45.9	5.68	2.54	0.000	0.000	0.000
AKIM mm.	0.196	3.55	6.27	8.87	96.9	155.	119.	15.2	6.59	0.000	0.000	0.000
MİL. M3	0.003	0.055	0.097	0.137	1.49	2.38	1.83	0.234	0.101	0.000	0.000	0.000

SU YILI (2006) YILLIK TOPLAM AKIM 6.33 MİLYON M3 411 MM. 13.0 LT/SN/Km2

07

BÜYÜK MENDERES HAVZASI

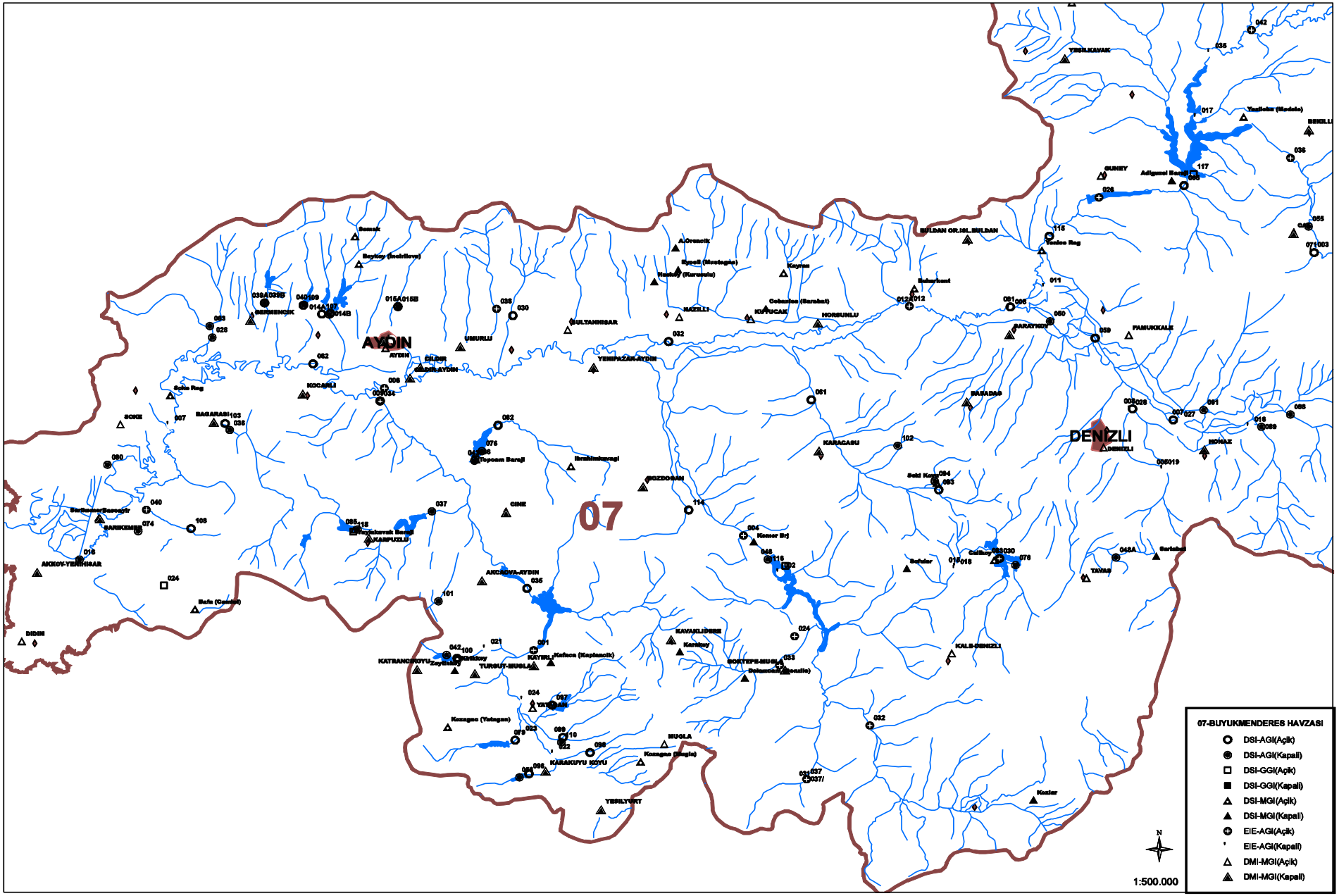
07
AYDIN
DENİZLI
07-BUYUKMENDERES HAVZASI
DSI-AGI(Açik)
DSI-AGI(Kapali)
DSI-GGI(Açik)
DSI-GGI(Kapali)
DSI-MGI(Açik)
DSI-MGI(Kapali)
EIE-AGI(Açik)
EIE-AGI(Kapali)
DMI-MGI(Açik)
DMI-MGI(Kapali)
N
1:500.000

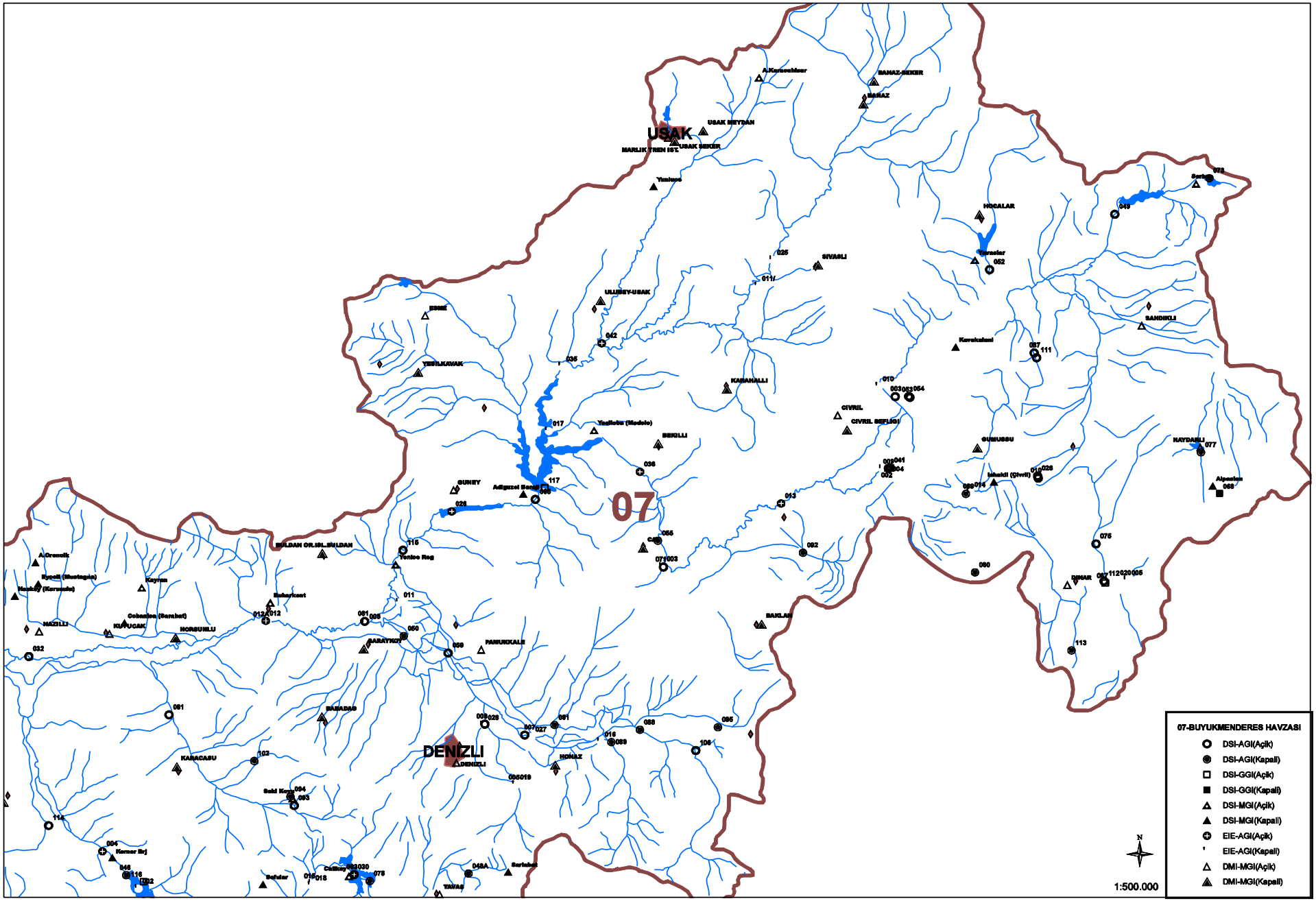
07
USAK
DENİZLI
07-BUYUKMENDERES HAVZASI
DSI-AGI(Açik)
DSI-AGI(Kapali)
DSI-GGI(Açik)
DSI-GGI(Kapali)
DSI-MGI(Açik)
DSI-MGI(Kapali)
EIE-AGI(Açik)
EIE-AGI(Kapali)
DMI-MGI(Açik)
DMI-MGI(Kapali)
N
1:500.000

07. Büyük Menderes Havzasi

D07A003 KUFİ ÇAYI IŞIKLI KÖPRÜSÜ

YERİ : **ÇİVRİL-IŞIKLI YOLU ÜZERİNDE ÇİVRİL'DEN 10 KM.MESAFEDE IŞIKLI KÖPRÜSÜNDEDİR.**
29°49'15" Doğu - 38°18'59" Kuzey

YAĞIŞ ALANI : **2015.00 km2** **YAKLAŞIK KOT : 837 m**

GÖZLEM SÜRESİ : **07.12.1958 - 30.09.2006**

ORTALAMA AKIMLAR : **Gözlem süresinde 2.543 m3/sn. (44 Yıllık) 2006 Su yılında 0.513 m3/sn.**

ANLIK EN ÇOK VE EN AZ AKIMLAR:

2006 Su yılında anlık ençok akım	**:**	**15.8**	**m3/sn**	**12.02.2006**
2006 Su yılında anlık enaz akım	**:**	**0.000**	**m3/sn**	**01.10.2005**
Gözlem süresinde anlık ençok akım	**:**	**230.**	**m3/sn**	**12.03.1968**
Gözlem süresinde anlık enaz akım	**:**	**0.000**	**m3/sn**	**21.04.1959**

8. Anahtar Eğrisi (Seviyeler cm olarak)

Seviye	Akım	Seviye	Akım	Seviye	Akım	Seviye	Akım
1	0.000	16	0.000	31	1.0	141	40.0
4	0.000	19	0.015	46	4.1	171	60.0
7	0.000	22	0.119	61	7.8	201	88.0
10	0.000	25	0.350	81	14.0	231	119.
13	0.000	28	0.630	111	25.0	261	155.

Akımlar 01 Ekim 2005 'den 30 Eylül 2006' a kadar m3/sn olarak

Gün	Ekim	Kasım	Aralık	Ocak	Şubat	Mart	Nisan	Mayıs	Haziran	Temmuz	Ağustos	Eylül
01	KURU	KURU	KURU	KURU	KURU	1.22	1.90	KURU	KURU	KURU	KURU	KURU
02	KURU	KURU	KURU	KURU	KURU	1.73	1.39	KURU	KURU	KURU	KURU	KURU
03	KURU	KURU	KURU	KURU	KURU	1.73	1.22	KURU	KURU	KURU	KURU	KURU
04	KURU	KURU	KURU	KURU	KURU	5.72	1.22	KURU	KURU	KURU	KURU	KURU
05	KURU	KURU	KURU	KURU	KURU	3.58	1.39	KURU	KURU	KURU	KURU	KURU
06	KURU	KURU	KURU	KURU	KURU	2.62	1.39	KURU	KURU	KURU	KURU	KURU
07	KURU	KURU	KURU	KURU	KURU	1.90	1.05	KURU	KURU	KURU	KURU	KURU
08	KURU	KURU	KURU	KURU	0.005	1.90	0.630	KURU	KURU	KURU	KURU	KURU
09	KURU	KURU	KURU	KURU	0.430	2.26	0.630	KURU	KURU	KURU	KURU	KURU
10	KURU	KURU	KURU	KURU	0.350	2.08	0.750	KURU	KURU	KURU	KURU	KURU
11	KURU	KURU	KURU	KURU	6.50	1.90	0.750	KURU	KURU	KURU	KURU	KURU
12	KURU	KURU	KURU	KURU	13.4	1.90	0.530	KURU	KURU	KURU	KURU	KURU
13	KURU	KURU	KURU	KURU	6.76	4.10	0.530	KURU	KURU	KURU	KURU	KURU
14	KURU	KURU	KURU	KURU	4.76	10.7	0.530	KURU	KURU	KURU	KURU	KURU
15	KURU	KURU	KURU	KURU	3.84	12.2	1.56	KURU	KURU	KURU	KURU	KURU
16	KURU	KURU	KURU	KURU	2.26	7.02	2.26	KURU	KURU	KURU	KURU	KURU
17	KURU	KURU	KURU	KURU	0.750	5.20	1.73	KURU	KURU	KURU	KURU	KURU
18	KURU	KURU	KURU	KURU	0.430	3.84	1.56	KURU	KURU	KURU	KURU	KURU
19	KURU	KURU	KURU	KURU	0.630	3.58	1.22	KURU	KURU	KURU	KURU	KURU
20	KURU	KURU	KURU	KURU	0.890	2.80	1.05	KURU	KURU	KURU	KURU	KURU
21	KURU	KURU	KURU	KURU	1.56	2.62	0.750	KURU	KURU	KURU	KURU	KURU
22	KURU	KURU	KURU	KURU	1.56	2.26	0.530	KURU	KURU	KURU	KURU	KURU
23	KURU	KURU	KURU	KURU	1.39	2.44	0.350	KURU	KURU	KURU	KURU	KURU
24	KURU	KURU	KURU	KURU	1.22	3.84	0.350	KURU	KURU	KURU	KURU	KURU
25	KURU	KURU	KURU	KURU	1.39	4.32	0.430	KURU	KURU	KURU	KURU	KURU
26	KURU	KURU	KURU	KURU	1.90	3.58	0.350	KURU	KURU	KURU	KURU	KURU
27	KURU	KURU	KURU	KURU	2.08	2.80	0.190	KURU	KURU	KURU	KURU	KURU
28	KURU	KURU	KURU	KURU	1.39	2.26	KURU	KURU	KURU	KURU	KURU	KURU
29	KURU	KURU	KURU	KURU	-----	1.73	KURU	KURU	KURU	KURU	KURU	KURU
30	KURU	KURU	KURU	KURU	-----	1.73	KURU	KURU	KURU	KURU	KURU	KURU
31	KURU	-----	KURU	KURU	-----	2.08	-----	KURU	-----	KURU	KURU	-----
Maks.	KURU	KURU	KURU	KURU	15.8	14.0	2.62	KURU	0.005	KURU	KURU	KURU
Min.	KURU	KURU	KURU	KURU	KURU	1.22	KURU	KURU	KURU	KURU	KURU	KURU
Ortalama	KURU	KURU	KURU	KURU	1.91	3.47	0.875	KURU	KURU	KURU	KURU	KURU
LT/SN/Km2	0.000	0.000	0.000	0.000	0.948	1.72	0.434	0.000	0.000	0.000	0.000	0.000
AKIM mm.	0.000	0.000	0.000	0.000	2.29	4.62	1.13	0.000	0.000	0.000	0.000	0.000
MİL. M3	0.000	0.000	0.000	0.000	4.62	9.30	2.27	0.000	0.000	0.000	0.000	0.000

SU YILI (2006) YILLIK TOPLAM AKIM 16.19 MİLYON M3 8 MM. 0.3 LT/SN/Km2

07. Büyük Menderes Havzasi

D07A008 GÖKPINAR ÇAYI AKHAN REGÜLATÖRÜ

YERİ : **DENİZLİ-DİNAR YOLUNUN 8.KM SİNDEKİ AKHAN KÖPRÜSÜ'NÜN MANSABINDADIR.**
29°8'13" Doğu - 37°49'5" Kuzey

YAĞIŞ ALANI : **265.00 km2** **YAKLAŞIK KOT : 290 m**

GÖZLEM SÜRESİ : **01.08.1978 - 30.09.2006**

ORTALAMA AKIMLAR : **Gözlem süresinde 1.960 m3/sn. (27 Yıllık) 2006 Su yılında 1.021 m3/sn.**

ANLIK EN ÇOK VE EN AZ AKIMLAR:

2006 Su yılında anlık ençok akım	**:**	**9.10 m3/sn**	**19.12.2005**
2006 Su yılında anlık enaz akım	**:**	**0.285 m3/sn**	**20.06.2006**
Gözlem süresinde anlık ençok akım	**:**	**30.0 m3/sn**	**18.01.1979**
Gözlem süresinde anlık enaz akım	**:**	**0.000 m3/sn**	**10.10.1989**

9. Anahtar Eğrisi (Seviyeler cm olarak)

Seviye	Akım	Seviye	Akım	Seviye	Akım	Seviye	Akım
28	0.035	70	2.3	140	11.8	190	19.8
30	0.055	80	3.5	150	13.3	200	21.4
40	0.311	100	6.0	160	14.9	210	23.0
50	0.804	120	8.8	170	16.6	220	24.6
60	1.5	130	10.3	180	18.2	230	26.4

Akımlar 01 Ekim 2005 'den 30 Eylül 2006' a kadar m3/sn olarak

Gün	Ekim	Kasım	Aralık	Ocak	Şubat	Mart	Nisan	Mayıs	Haziran	Temmuz	Ağustos	Eylül
01	0.891	1.23	0.835	0.890	0.890	1.00	1.00	1.00	0.725	0.725	1.00	1.24
02	1.30	1.37	0.835	0.890	0.890	0.890	0.945	0.780	0.725	0.615	1.08	1.24
03	1.17	1.74	0.835	0.890	0.890	0.890	0.945	0.780	0.670	0.780	1.08	1.24
04	1.10	1.52	0.835	0.945	0.890	0.890	1.00	1.56	0.670	1.08	1.08	0.890
05	1.10	1.30	0.780	1.56	0.835	0.890	1.00	0.835	0.670	1.00	1.08	0.670
06	1.10	1.30	0.835	0.945	1.56	0.890	0.945	0.835	0.670	0.945	1.08	0.780
07	1.10	1.30	0.835	0.890	1.24	0.945	0.945	0.780	0.670	0.945	1.16	0.780
08	1.10	1.52	0.835	0.890	1.16	1.89	0.945	0.835	0.670	0.945	1.24	0.890
09	1.10	1.74	0.835	0.835	1.00	1.08	0.945	0.890	0.890	0.835	1.16	0.835
10	1.10	1.74	0.835	0.835	1.08	0.945	0.945	0.835	0.890	0.835	1.16	0.890
11	1.10	1.74	0.835	0.835	1.16	0.945	0.890	0.835	0.890	0.835	1.16	0.835
12	1.10	1.74	0.780	0.835	1.24	0.945	0.835	0.835	0.890	0.945	1.16	0.835
13	1.10	1.82	0.835	0.835	0.945	1.72	0.835	0.835	1.00	1.08	1.08	0.780
14	1.10	1.82	0.835	0.835	0.945	4.02	1.32	0.835	0.835	0.945	1.08	0.835
15	1.17	1.82	0.890	0.835	0.945	3.36	0.945	0.835	0.835	0.945	1.16	0.835
16	1.17	1.82	0.780	0.835	0.945	2.70	0.890	0.945	0.725	0.945	1.24	0.780
17	1.17	1.90	0.780	0.835	0.945	2.16	0.835	0.835	0.560	0.890	1.24	0.835
18	1.23	2.07	1.16	0.835	0.945	2.07	0.835	0.835	0.450	0.890	1.24	0.780
19	1.23	1.24	3.36	1.00	0.945	1.72	0.890	0.780	0.384	0.890	1.16	0.835
20	1.44	1.08	1.80	1.24	0.890	1.64	0.835	0.780	0.450	0.890	1.16	0.835
21	2.20	0.945	0.945	0.890	0.890	1.56	0.725	0.725	0.780	0.945	1.16	0.780
22	1.82	0.780	0.945	0.890	0.890	1.40	0.670	0.560	0.835	0.890	1.16	0.780
23	1.23	0.780	0.945	0.945	0.890	1.24	0.890	0.615	0.835	0.890	1.24	0.890
24	1.17	0.835	0.945	1.24	0.890	1.16	0.670	0.615	0.835	0.890	1.24	0.890
25	1.23	0.890	0.945	1.48	0.945	1.08	0.560	0.560	0.835	0.945	1.24	0.560
26	1.23	1.48	0.945	1.00	1.00	1.00	0.615	0.615	0.890	0.945	1.16	0.560
27	1.30	0.835	0.890	0.945	0.835	1.00	0.725	0.560	0.670	1.08	1.16	0.560
28	1.30	0.835	0.890	0.890	0.890	1.00	0.890	0.560	0.780	1.00	1.16	0.615
29	1.30	0.835	0.945	0.890	-----	1.00	0.945	0.615	0.780	1.00	1.24	0.615
30	1.30	0.835	0.945	0.890	-----	1.00	1.00	0.615	0.780	1.00	1.32	0.560
31	1.23	-----	0.945	0.890	-----	1.00	-----	0.670	-----	1.00	1.08	-----
Maks.	2.20	8.35	9.10	4.46	5.38	7.90	4.35	7.90	6.82	3.80	1.48	3.91
Min.	0.891	0.670	0.725	0.725	0.780	0.780	0.450	0.417	0.285	0.560	0.945	0.450
Ortalama	1.23	1.36	0.988	0.950	0.985	1.42	0.881	0.780	0.743	0.921	1.16	0.815
LT/SN/Km2	4.65	5.14	3.73	3.58	3.72	5.36	3.32	2.94	2.80	3.47	4.38	3.08
AKIM mm.	12.4	13.3	9.99	9.60	8.99	14.4	8.61	7.89	7.27	9.31	11.7	7.97
MİL. M3	3.30	3.53	2.65	2.54	2.38	3.80	2.28	2.09	1.93	2.47	3.11	2.11

SU YILI (2006) YILLIK TOPLAM AKIM 32.19 MİLYON M3 121 MM. 3.9 LT/SN/Km2

07. Büyük Menderes Havzasi

D07A009 ÇİNE Ç. ÇAKIRBEYLİ KÖPRÜSÜ

YERİ : **AYDIN-CINE YOLUNUN 12.KM DEN CAKIRBEYLI KOYUNE GIDEN YOLUN UZERINDEKI ÇİNE ÇAYI KÖP.20M MENBASINDADIR.**
27°50'6" Doğu - 37°45'45" Kuzey

YAĞIŞ ALANI : **2750.00 km2** **YAKLAŞIK KOT : 28 m**

GÖZLEM SÜRESİ : **01.10.1962 - 30.09.2006**

ORTALAMA AKIMLAR : **Gözlem süresinde 10.636 m3/sn. (24 Yıllık) 2006 Su yılında 12.155 m3/sn.**

ANLIK EN ÇOK VE EN AZ AKIMLAR:

2006 Su yılında anlık ençok akım	:	**323.**	**m3/sn**	**14.03.2006**
2006 Su yılında anlık enaz akım	:	**0.002**	**m3/sn**	**01.10.2005**
Gözlem süresinde anlık ençok akım	:	**970.**	**m3/sn**	**04.02.1978**
Gözlem süresinde anlık enaz akım	:	**0.000**	**m3/sn**	**07.08.1967**

Akımlar 01 Ekim 2005 'den 30 Eylül 2006' a kadar m3/sn olarak

Gün	Ekim	Kasım	Aralık	Ocak	Şubat	Mart	Nisan	Mayıs	Haziran	Temmuz	Ağustos	Eylül
01	0.173	1.31	5.50	7.67	8.33	13.3	15.1	7.39	2.26	0.559	6.84	0.311
02	4.16	1.31	4.85	7.39	8.33	13.9	14.7	7.67	2.26	0.404	7.39	0.373
03	11.3	1.31	4.46	6.29	7.89	13.1	14.4	7.12	2.05	0.528	7.67	0.342
04	4.16	1.41	4.27	6.03	7.44	13.3	14.0	6.84	1.84	1.20	4.85	0.280
05	2.42	1.41	3.87	5.76	6.99	12.8	15.1	7.39	1.84	7.39	6.84	0.373
06	1.73	1.52	3.87	14.0	11.9	12.2	14.4	7.12	1.84	4.65	7.12	0.404
07	1.41	1.52	3.69	13.0	94.8	10.6	13.3	6.84	1.94	2.15	7.12	0.342
08	1.31	1.62	3.69	12.6	121.	57.5	12.3	6.56	1.94	1.52	7.12	0.311
09	1.20	1.62	3.69	9.90	67.4	162.	11.6	6.56	1.84	1.14	4.65	0.311
10	1.14	1.52	3.69	8.28	38.2	86.4	11.6	6.29	1.94	1.02	6.03	0.311
11	1.14	1.52	3.51	7.39	103.	37.6	11.2	6.29	2.05	0.834	6.84	0.259
12	1.14	1.62	3.33	6.56	206.	24.7	10.9	6.29	2.44	0.773	6.84	0.159
13	1.14	1.62	3.33	6.03	120.	113.	10.2	6.56	1.94	1.14	6.84	0.280
14	1.20	1.52	3.33	5.76	66.1	259.	10.2	6.29	1.84	5.04	6.84	0.410
15	1.14	1.52	3.51	5.50	36.4	205.	14.0	5.76	1.73	5.50	5.23	0.497
16	1.08	1.52	5.23	5.23	22.5	102.	13.0	5.50	1.73	5.65	3.51	0.466
17	1.02	1.52	4.85	5.04	18.7	68.6	11.2	5.50	1.41	4.46	2.97	0.342
18	1.14	2.15	4.85	4.85	20.3	58.9	10.2	5.50	1.20	4.27	2.97	0.237
19	1.31	5.79	43.1	5.76	20.7	57.5	9.90	5.23	1.08	3.51	2.97	0.144
20	1.41	5.00	58.2	29.7	19.0	36.5	9.58	5.04	1.08	2.62	2.80	0.237
21	1.31	6.57	15.1	17.0	16.7	27.0	9.25	5.04	0.834	1.84	2.80	0.773
22	1.31	4.48	9.90	11.6	14.8	25.6	8.93	4.65	1.02	1.41	2.62	0.956
23	1.20	3.52	7.95	12.6	13.9	23.7	10.6	4.65	1.94	1.20	1.14	0.528
24	1.20	3.04	6.84	20.2	12.8	22.8	9.25	4.46	1.14	1.84	0.497	0.404
25	1.20	3.36	6.03	85.9	12.5	21.5	8.60	4.27	0.895	5.50	0.373	2.26
26	1.31	50.4	5.23	58.7	12.8	20.7	8.28	4.27	0.712	6.56	0.311	2.62
27	1.31	57.5	5.04	18.0	13.3	18.5	7.95	3.69	1.41	6.84	0.259	1.41
28	1.31	12.3	4.85	13.1	11.9	17.4	8.67	3.33	1.62	7.12	0.237	1.02
29	1.41	8.28	4.85	10.8	-----	16.2	8.67	2.97	1.20	7.39	0.311	0.834
30	1.20	6.56	7.12	9.52	-----	15.5	8.67	2.80	0.895	6.03	0.342	0.956
31	1.20	-----	6.84	8.55	-----	15.1	-----	2.26	-----	4.05	0.342	-----
Maks.	24.4	165.	194.	146.	221.	323.	16.2	8.28	2.62	10.6	8.60	5.76
Min.	0.002	1.31	3.33	4.85	6.77	10.0	7.39	2.26	0.651	0.404	0.194	0.144
Ortalama	1.76	6.48	8.21	14.2	39.8	51.0	11.2	5.49	1.60	3.36	3.96	0.605
LT/SN/Km2	0.641	2.36	2.99	5.15	14.5	18.6	4.07	2.00	0.581	1.22	1.44	0.220
AKIM mm.	1.72	6.11	8.00	13.8	35.0	49.7	10.5	5.35	1.51	3.27	3.85	0.570
MİL. M3	4.72	16.8	22.0	37.9	96.2	137.	29.0	14.7	4.14	9.00	10.6	1.57

SU YILI (2006) YILLIK TOPLAM AKIM 383.63 MİLYON M3 140 MM. 4.4 LT/SN/Km2

07. Büyük Menderes Havzasi

D07A010 DİNAR SUYU IRGILLI REGÜLATÖR ÇIKIŞI

YERİ : **DİNAR-HOMA YOLUNUN 9.KM.DEKİ IRGILLI REG.300.M.MANSABINDADIR.**
30°6'0" Doğu - 38°7'0" Kuzey

YAĞIŞ ALANI : **295.70 km2** **YAKLAŞIK KOT : 841 m**

GÖZLEM SÜRESİ : **01.10.1960 - 30.09.2006**

ORTALAMA AKIMLAR : **Gözlem süresinde 2.213 m3/sn. (43 Yıllık) 2006 Su yılında 1.518 m3/sn.**

ANLIK EN ÇOK VE EN AZ AKIMLAR:

2006 Su yılında anlık ençok akım	:	**3.82**	**m3/sn**	**02.10.2005**
2006 Su yılında anlık enaz akım	:	**0.005**	**m3/sn**	**30.08.2006**
Gözlem süresinde anlık ençok akım	:	**52.1**	**m3/sn**	**02.09.1997**
Gözlem süresinde anlık enaz akım	:	**0.000**	**m3/sn**	**11.08.1986**

8. Anahtar Eğrisi (Seviyeler cm olarak)

Seviye	Akım	Seviye	Akım	Seviye	Akım	Seviye	Akım
3	0.000	13	0.185	30	0.940	70	4.0
5	0.005	15	0.260	35	1.2	80	5.0
7	0.033	17	0.330	40	1.6	90	6.0
9	0.075	19	0.410	50	2.3	100	7.2
11	0.125	25	0.670	60	3.1	110	8.4

Akımlar 01 Ekim 2005 'den 30 Eylül 2006' a kadar m3/sn olarak

Gün	Ekim	Kasım	Aralık	Ocak	Şubat	Mart	Nisan	Mayıs	Haziran	Temmuz	Ağustos	Eylül
01	0.670	2.38	2.46	2.38	1.39	2.62	2.70	1.32	0.330	0.017	0.033	0.005
02	1.81	2.38	2.46	2.38	1.60	2.62	2.70	1.19	0.330	0.033	0.033	0.005
03	2.30	2.46	2.38	2.46	2.70	2.62	2.70	1.19	0.260	0.033	0.033	0.005
04	2.30	2.62	2.46	2.38	2.62	2.70	2.62	1.19	0.185	0.033	0.033	0.005
05	2.23	2.54	2.38	2.38	2.62	2.70	2.54	1.46	0.052	0.033	0.033	0.005
06	2.23	2.54	2.38	2.38	2.70	2.62	2.54	1.46	0.017	0.033	0.033	0.005
07	2.16	2.54	2.38	1.60	2.70	2.62	2.62	1.60	0.017	0.033	0.033	0.005
08	2.16	2.38	2.38	1.46	2.78	2.78	2.62	1.67	0.017	0.033	0.033	0.005
09	2.16	2.30	2.38	1.46	2.78	2.86	2.54	1.60	0.017	0.033	0.033	0.005
10	2.16	2.30	2.38	1.39	2.70	2.78	2.54	1.53	0.017	0.033	0.033	0.005
11	2.16	2.30	2.38	1.39	2.70	2.70	2.54	1.53	0.017	0.033	0.033	0.005
12	2.23	2.30	2.38	1.39	2.70	2.70	2.54	1.53	0.017	0.033	0.033	0.005
13	2.30	2.30	2.38	1.39	2.70	2.94	2.62	1.53	0.017	0.033	0.033	0.005
14	2.23	2.30	2.38	1.39	2.70	2.86	2.70	1.53	0.017	0.033	0.033	0.005
15	2.30	2.30	2.46	1.39	2.70	2.78	2.70	1.53	0.017	0.033	0.033	0.005
16	2.30	2.30	2.54	1.39	2.62	2.70	2.62	1.60	0.017	0.033	0.017	0.005
17	2.30	2.30	2.54	1.39	2.62	2.78	2.62	1.60	0.017	0.033	0.017	0.005
18	2.30	2.38	2.54	1.46	2.62	2.70	2.54	1.53	0.017	0.033	0.017	0.005
19	2.38	2.46	2.54	1.46	2.62	2.70	2.54	1.53	0.017	0.033	0.017	0.005
20	2.30	2.62	2.54	2.86	2.62	2.62	2.54	1.53	0.017	0.033	0.017	0.005
21	2.30	2.62	2.46	2.54	2.62	2.70	2.54	1.53	0.017	0.033	0.017	0.005
22	2.30	2.62	2.46	2.54	2.62	2.70	2.54	1.53	0.017	0.033	0.017	0.005
23	2.23	2.54	2.46	2.62	2.62	2.70	2.62	0.940	0.017	0.033	0.017	0.005
24	2.30	2.54	2.46	2.62	2.62	2.70	2.70	0.260	0.017	0.033	0.017	0.005
25	2.38	2.46	2.38	2.62	2.62	2.78	2.46	0.260	0.017	0.033	0.017	0.005
26	2.38	2.54	2.38	2.54	2.62	2.70	2.54	0.778	0.017	0.033	0.017	0.005
27	2.38	2.54	2.38	2.54	2.70	2.70	2.46	1.74	0.017	0.033	0.017	0.005
28	2.46	2.46	2.38	2.46	2.62	2.70	2.38	1.60	0.017	0.033	0.017	0.005
29	2.38	2.46	2.46	2.30	-----	2.62	2.30	0.330	0.017	0.033	0.017	0.005
30	2.46	2.46	2.46	1.39	-----	2.70	1.46	0.330	0.017	0.033	0.005	0.005
31	2.38	-----	2.38	1.39	-----	2.70	-----	0.330	-----	0.033	0.005	-----
Maks.	3.82	2.86	2.78	3.19	3.10	3.55	3.64	2.30	0.330	0.033	0.033	0.005
Min.	0.670	2.16	2.30	1.32	1.39	2.62	1.39	0.185	0.017	0.017	0.005	0.005
Ortalama	2.22	2.44	2.43	1.98	2.58	2.71	2.54	1.27	0.053	0.032	0.024	0.005
LT/SN/Km2	7.52	8.26	8.22	6.69	8.72	9.17	8.58	4.28	0.178	0.110	0.081	0.017
AKIM mm.	20.1	21.4	22.0	17.9	21.1	24.6	22.2	11.5	0.462	0.294	0.217	0.044
MİL. M3	5.96	6.33	6.51	5.30	6.24	7.27	6.57	3.39	0.137	0.087	0.064	0.013

SU YILI (2006) YILLIK TOPLAM AKIM 47.87 MİLYON M3 162 MM. 5.1 LT/SN/Km2

07. Büyük Menderes Havzasi

D07A014 İKİZDERE DEREAĞZI

YERİ : **AYDINA 10 KM. DEKİ İNCİRLİOVA-İKİZDERE BARAJI'NA 200 M. KALA, YOLUN ALTINDADIR. 27°44'0" Doğu - 37°53'0" Kuzey**

YAĞIŞ ALANI : **165.00 km2** **YAKLAŞIK KOT : 67 m**

GÖZLEM SÜRESİ : **01.10.1968 - 30.09.2006**

ORTALAMA AKIMLAR : **Gözlem süresinde 2.529 m3/sn. (35 Yıllık) 2006 Su yılında 2.529 m3/sn.**

ANLIK EN ÇOK VE EN AZ AKIMLAR:

2006 Su yılında anlık ençok akım	:	**55.5**	**m3/sn**	**26.11.2005**
2006 Su yılında anlık enaz akım	:	**0.012**	**m3/sn**	**31.08.2006**
Gözlem süresinde anlık ençok akım	:	**420.**	**m3/sn**	**11.11.1980**
Gözlem süresinde anlık enaz akım	:	**0.000**	**m3/sn**	**01.10.1968**

24. Anahtar Eğrisi (Seviyeler cm olarak)

Seviye	Akım	Seviye	Akım	Seviye	Akım	Seviye	Akım
1	0.000	26	0.051	111	33.3	261	176.
4	0.000	36	0.296	141	60.3	291	206.
7	0.000	51	1.6	171	87.3	321	236.
10	0.001	66	4.9	201	116.	351	266.
16	0.007	81	11.3	231	146.		

Akımlar 01 Ekim 2005 'den 30 Eylül 2006' a kadar m3/sn olarak

Gün	Ekim	Kasım	Aralık	Ocak	Şubat	Mart	Nisan	Mayıs	Haziran	Temmuz	Ağustos	Eylül
01	1.50	0.480	1.10	1.96	2.19	9.50	2.19	0.768	0.840	0.078	0.026	0.012
02	2.65	0.552	0.840	1.50	2.19	9.50	1.96	0.768	0.972	0.078	0.026	0.012
03	1.10	0.624	0.768	1.37	1.73	9.50	1.96	0.696	0.696	0.078	0.026	0.012
04	1.10	0.696	0.768	1.24	1.73	9.50	1.96	0.696	0.126	0.360	0.026	0.012
05	1.10	0.696	0.696	1.37	1.50	9.50	1.96	0.696	0.480	0.360	0.026	0.012
06	0.972	0.696	0.696	1.96	2.88	9.50	1.96	0.696	0.552	0.126	0.026	0.012
07	0.840	0.624	0.696	1.73	3.80	12.0	1.96	0.624	0.624	0.090	0.021	0.012
08	0.840	0.624	0.696	1.73	4.12	15.0	1.96	0.624	0.552	0.090	0.021	0.012
09	0.840	0.696	0.696	1.50	3.57	13.8	1.96	0.624	0.696	0.078	0.021	0.012
10	0.972	0.624	0.624	1.37	15.0	12.0	1.50	0.624	0.972	0.066	0.021	0.012
11	0.972	0.696	0.552	1.24	47.0	10.0	1.50	0.552	0.768	0.066	0.030	0.012
12	0.972	0.696	0.552	1.24	29.6	10.0	1.50	0.552	0.768	0.066	0.030	0.012
13	0.972	0.624	0.552	1.10	21.0	9.50	1.50	0.552	0.768	0.066	0.026	0.012
14	0.972	0.624	0.552	1.10	16.2	18.0	1.50	0.480	0.768	0.066	0.021	0.012
15	0.972	0.624	0.696	0.972	11.0	10.0	1.50	0.480	0.624	0.066	0.021	0.012
16	0.972	0.624	0.696	0.972	9.50	6.68	1.37	0.480	0.480	0.066	0.021	0.012
17	0.972	0.768	0.696	0.972	9.00	6.04	1.37	0.480	0.360	0.054	0.021	0.012
18	0.972	6.36	0.768	0.840	7.00	6.04	1.37	0.420	0.240	0.054	0.021	0.012
19	0.768	3.34	1.73	9.50	8.00	6.04	1.37	0.420	0.180	0.054	0.021	0.012
20	0.624	7.00	1.37	27.5	7.50	5.72	1.37	0.552	0.144	0.054	0.021	0.012
21	0.624	3.11	1.10	18.0	7.00	5.72	1.37	1.10	0.126	0.042	0.017	0.012
22	0.624	1.50	0.840	15.0	7.00	3.34	1.37	1.10	0.108	0.042	0.017	0.012
23	0.624	1.73	0.840	3.80	7.00	3.80	1.37	1.37	0.108	0.042	0.017	0.012
24	0.624	2.88	0.768	3.80	7.00	3.80	1.37	1.50	0.108	0.042	0.017	0.012
25	0.624	3.11	0.768	6.68	7.00	3.80	1.37	1.24	0.090	0.042	0.017	0.021
26	0.624	41.4	0.696	5.40	8.50	3.34	0.972	0.972	0.090	0.030	0.017	0.026
27	0.624	29.6	0.768	4.12	9.50	2.88	0.840	0.840	0.090	0.030	0.017	0.026
28	0.552	28.9	0.768	3.57	9.50	2.65	0.840	0.840	0.090	0.030	0.017	0.026
29	0.480	11.5	0.840	3.34	-----	2.42	0.840	0.768	0.090	0.030	0.017	0.090
30	0.480	1.24	0.840	3.11	-----	2.42	0.768	1.37	0.078	0.030	0.017	0.360
31	0.480	-----	1.50	2.88	-----	2.19	-----	1.10	-----	0.030	0.012	-----
Maks.	4.12	55.5	2.88	27.5	47.0	19.2	2.19	2.42	1.37	1.10	0.030	0.360
Min.	0.480	0.480	0.480	0.840	1.50	2.19	0.768	0.180	0.054	0.017	0.012	0.012
Ortalama	0.885	5.09	0.822	4.22	9.54	7.55	1.49	0.774	0.420	0.078	0.021	0.028
LT/SN/Km2	5.37	30.8	4.98	25.6	57.8	45.8	9.06	4.69	2.54	0.470	0.128	0.169
AKIM mm.	14.4	79.9	13.3	68.5	140.	123.	23.5	12.6	6.59	1.26	0.343	0.438
MİL. M3	2.37	13.2	2.20	11.3	23.1	20.2	3.87	2.07	1.09	0.208	0.057	0.072

SU YILI (2006) YILLIK TOPLAM AKIM 79.74 MİLYON M3 483 MM. 15.3 LT/SN/Km2

07. Büyük Menderes Havzasi

D07A015 TABAKHANE DERSİ. AYDIN-TERSİP BENDI

YERİ : **AYDIN A 6.5.KM. MESAFEDEKİ BELEDİYE TERSİP HAVUZLARININ YANINDAKİ KÖPRÜNÜN 15 M MANSABINDADIR.**
27°51'8" Doğu - 37°53'56" Kuzey

YAĞIŞ ALANI : **54.00 km2** **YAKLAŞIK KOT : 231 m**

GÖZLEM SÜRESİ : **01.07.1985 - 30.09.2006**

ORTALAMA AKIMLAR : **Gözlem süresinde 0.458 m3/sn. (9 Yıllık) 2006 Su yılında 0.740 m3/sn.**

ANLIK EN ÇOK VE EN AZ AKIMLAR:

2006 Su yılında anlık ençok akım	**:**	**16.5**	**m3/sn**	**11.02.2006**
2006 Su yılında anlık enaz akım	**:**	**0.000**	**m3/sn**	**01.10.2005**
Gözlem süresinde anlık ençok akım	**:**	**35.0**	**m3/sn**	**28.12.1960**
Gözlem süresinde anlık enaz akım	**:**	**0.000**	**m3/sn**	**30.01.1989**

Akımlar 01 Ekim 2005 'den 30 Eylül 2006' a kadar m3/sn olarak

Gün	Ekim	Kasım	Aralık	Ocak	Şubat	Mart	Nisan	Mayıs	Haziran	Temmuz	Ağustos	Eylül
01	KURU	KURU	0.170	1.80	1.53	1.26	0.420	KURU	KURU	KURU	KURU	KURU
02	KURU	KURU	0.020	1.04	1.39	1.26	0.170	KURU	KURU	KURU	KURU	KURU
03	KURU	KURU	KURU	0.784	1.04	1.26	0.125	KURU	KURU	KURU	KURU	KURU
04	KURU	KURU	KURU	0.784	0.630	0.784	0.125	KURU	KURU	KURU	KURU	KURU
05	KURU	KURU	KURU	1.26	0.784	0.630	0.125	KURU	KURU	KURU	KURU	KURU
06	KURU	KURU	KURU	0.784	3.13	0.170	0.041	KURU	KURU	KURU	KURU	KURU
07	KURU	KURU	KURU	0.700	4.15	0.260	0.041	KURU	KURU	KURU	KURU	KURU
08	KURU	KURU	KURU	0.700	3.98	2.96	0.012	KURU	KURU	KURU	KURU	KURU
09	KURU	KURU	KURU	0.630	3.81	3.30	0.018	KURU	KURU	KURU	KURU	KURU
10	KURU	KURU	KURU	0.170	5.90	2.96	0.018	KURU	KURU	KURU	KURU	KURU
11	KURU	KURU	KURU	0.125	14.9	2.96	0.018	KURU	KURU	KURU	KURU	KURU
12	KURU	KURU	KURU	0.125	9.17	2.79	0.018	KURU	KURU	KURU	KURU	KURU
13	KURU	KURU	KURU	0.125	7.70	4.66	0.018	KURU	KURU	KURU	KURU	KURU
14	KURU	KURU	KURU	0.083	5.54	6.62	0.018	KURU	KURU	KURU	KURU	KURU
15	KURU	KURU	KURU	0.062	5.00	6.44	0.018	KURU	KURU	KURU	KURU	KURU
16	KURU	KURU	KURU	0.012	4.66	5.54	0.018	KURU	KURU	KURU	KURU	KURU
17	KURU	0.018	KURU	KURU	3.81	5.18	0.018	KURU	KURU	KURU	KURU	KURU
18	KURU	2.96	0.014	KURU	3.64	5.00	0.014	KURU	KURU	KURU	KURU	KURU
19	KURU	0.041	0.490	3.81	3.64	4.32	0.014	KURU	KURU	KURU	KURU	KURU
20	KURU	0.490	0.062	8.24	3.30	3.98	0.014	KURU	KURU	KURU	KURU	KURU
21	KURU	0.012	0.041	7.34	3.30	3.30	0.014	KURU	KURU	KURU	KURU	KURU
22	KURU	KURU	0.012	3.64	3.13	3.30	0.014	KURU	KURU	KURU	KURU	KURU
23	KURU	KURU	0.012	3.30	1.93	3.30	0.014	KURU	KURU	KURU	KURU	KURU
24	KURU	KURU	0.012	3.30	1.80	3.30	0.014	KURU	KURU	KURU	KURU	KURU
25	KURU	0.041	0.012	3.30	1.80	2.62	0.014	KURU	KURU	KURU	KURU	KURU
26	KURU	6.08	0.012	3.81	1.80	2.45	0.014	KURU	KURU	KURU	KURU	KURU
27	KURU	2.96	KURU	3.47	1.66	1.53	KURU	KURU	KURU	KURU	KURU	KURU
28	KURU	2.45	KURU	2.96	0.784	1.26	KURU	KURU	KURU	KURU	KURU	KURU
29	KURU	1.12	KURU	2.32	-----	1.12	KURU	KURU	KURU	KURU	KURU	KURU
30	KURU	0.952	0.016	2.32	-----	0.630	KURU	KURU	KURU	KURU	KURU	KURU
31	KURU	-----	2.32	1.80	-----	0.490	-----	KURU	-----	KURU	KURU	-----
Maks.	KURU	6.08	2.96	12.5	16.5	6.80	0.420	KURU	KURU	KURU	KURU	KURU
Min.	KURU	KURU	KURU	KURU	0.560	0.170	KURU	KURU	KURU	KURU	KURU	KURU
Ortalama	KURU	0.571	0.103	1.90	3.71	2.76	0.045	KURU	KURU	KURU	KURU	KURU
LT/SN/Km2	0.000	10.6	1.91	35.1	68.7	51.2	0.831	0.000	0.000	0.000	0.000	0.000
AKIM mm.	0.000	27.4	5.11	94.1	166.	137.	2.16	0.000	0.000	0.000	0.000	0.000
MİL. M3	0.000	1.48	0.276	5.08	8.98	7.40	0.116	0.000	0.000	0.000	0.000	0.000

SU YILI (2006) YILLIK TOPLAM AKIM 23.33 MİLYON M3 432 MM. 13.7 LT/SN/Km2

07. Büyük Menderes Havzasi

D07A026 DİNAR SUYU. IRGILLI SULAMA KANALI.

YERİ : **DİNAR-HOMA BUCAĞI YOLUNUN 9.KM. DEKİ IRGILLI REG.NİN MANSABINDADIR.**
30°5'43" Doğu - 38°7'13" Kuzey

YAĞIŞ ALANI : **293.00 km2** **YAKLAŞIK KOT : 841 m**

GÖZLEM SÜRESİ : **27.03.1961 - 30.09.2006**

ORTALAMA AKIMLAR : **Gözlem süresinde 0.691 m3/sn. (23 Yıllık) 2006 Su yılında 0.388 m3/sn.**

ANLIK EN ÇOK VE EN AZ AKIMLAR:

2006 Su yılında anlık ençok akım	:	**2.50**	**m3/sn**	**23.09.2006**
2006 Su yılında anlık enaz akım	:	**0.000**	**m3/sn**	**24.10.2005**
Gözlem süresinde anlık ençok akım	:	**5.20**	**m3/sn**	**07.08.1983**
Gözlem süresinde anlık enaz akım	:	**0.000**	**m3/sn**	**01.10.1967**

Akımlar 01 Ekim 2005 'den 30 Eylül 2006' a kadar m3/sn olarak

Gün	Ekim	Kasım	Aralık	Ocak	Şubat	Mart	Nisan	Mayıs	Haziran	Temmuz	Ağustos	Eylül
01	1.30	KURU	KURU	KURU	KURU	KURU	KURU	KURU	0.660	0.860	1.00	1.25
02	0.420	KURU	KURU	KURU	KURU	KURU	KURU	KURU	0.690	0.910	1.00	1.25
03	0.195	KURU	KURU	KURU	KURU	KURU	KURU	KURU	0.690	0.910	1.10	1.25
04	0.180	KURU	KURU	KURU	KURU	KURU	KURU	KURU	0.720	1.00	1.20	1.25
05	0.180	KURU	KURU	KURU	KURU	KURU	KURU	KURU	0.800	1.00	1.43	1.05
06	0.180	KURU	KURU	KURU	KURU	KURU	KURU	KURU	0.800	0.980	1.33	1.10
07	0.180	KURU	KURU	KURU	KURU	KURU	KURU	KURU	0.720	0.980	1.15	1.35
08	0.180	KURU	KURU	KURU	KURU	KURU	KURU	KURU	0.800	0.960	1.00	1.75
09	0.180	KURU	KURU	KURU	KURU	KURU	KURU	KURU	0.800	0.960	1.00	1.75
10	0.180	KURU	KURU	KURU	KURU	KURU	KURU	KURU	0.830	0.960	1.05	1.70
11	0.180	KURU	KURU	KURU	KURU	KURU	KURU	KURU	0.910	0.910	1.05	1.75
12	0.160	KURU	KURU	KURU	KURU	KURU	KURU	KURU	0.830	0.860	1.00	1.75
13	0.160	KURU	KURU	KURU	KURU	KURU	KURU	KURU	0.830	0.910	1.00	1.75
14	0.160	KURU	KURU	KURU	KURU	KURU	KURU	KURU	0.830	0.860	1.00	1.80
15	0.160	KURU	KURU	KURU	KURU	KURU	KURU	KURU	0.910	0.960	1.20	1.80
16	0.160	KURU	KURU	KURU	KURU	KURU	KURU	KURU	1.00	0.860	1.25	1.80
17	0.160	KURU	KURU	KURU	KURU	KURU	KURU	KURU	0.960	0.960	1.30	1.80
18	0.160	KURU	KURU	KURU	KURU	KURU	KURU	KURU	0.860	0.980	1.33	1.80
19	0.160	KURU	KURU	KURU	KURU	KURU	KURU	KURU	0.960	0.910	1.70	1.80
20	0.160	KURU	KURU	KURU	KURU	KURU	KURU	KURU	0.980	0.980	1.43	1.80
21	0.145	KURU	KURU	KURU	KURU	KURU	KURU	KURU	0.910	0.910	1.50	2.03
22	0.145	KURU	KURU	KURU	KURU	KURU	KURU	KURU	0.830	0.860	1.50	2.10
23	0.145	KURU	KURU	KURU	KURU	KURU	KURU	0.029	0.830	0.830	1.50	1.43
24	0.020	KURU	KURU	KURU	KURU	KURU	KURU	0.480	0.830	0.800	1.53	0.830
25	KURU	KURU	KURU	KURU	KURU	KURU	KURU	0.510	0.830	0.800	1.70	0.310
26	KURU	KURU	KURU	KURU	KURU	KURU	KURU	0.160	0.860	0.910	1.75	0.310
27	KURU	KURU	KURU	KURU	KURU	KURU	KURU	0.013	0.830	0.860	1.75	0.100
28	KURU	KURU	KURU	KURU	KURU	KURU	KURU	0.009	0.910	0.960	1.70	0.080
29	KURU	KURU	KURU	KURU	-----	KURU	KURU	0.450	0.980	0.980	1.70	0.080
30	KURU	KURU	KURU	KURU	-----	KURU	KURU	0.450	0.960	0.910	1.65	0.080
31	KURU	-----	KURU	KURU	-----	KURU	-----	0.510	-----	0.980	1.30	-----
Maks.	1.30	KURU	KURU	KURU	KURU	KURU	KURU	0.630	1.15	1.10	2.15	2.50
Min.	KURU	KURU	KURU	KURU	KURU	KURU	KURU	KURU	0.135	0.570	0.760	0.029
Ortalama	0.169	KURU	KURU	KURU	KURU	KURU	KURU	0.084	0.845	0.920	1.33	1.30
LT/SN/Km2	0.578	0.000	0.000	0.000	0.000	0.000	0.000	0.287	2.88	3.14	4.52	4.43
AKIM mm.	1.55	0.000	0.000	0.000	0.000	0.000	0.000	0.770	7.48	8.41	12.1	11.5
MİL. M3	0.454	0.000	0.000	0.000	0.000	0.000	0.000	0.226	2.19	2.46	3.55	3.36

SU YILI (2006) YILLIK TOPLAM AKIM 12.24 MİLYON M3 42 MM. 1.3 LT/SN/Km2

07. Büyük Menderes Havzasi

D07A030 KÖŞK DERESİ MEZEKÖY

YERİ : **AYDIN-NAZİLLİ YOLUNUN 21.KM.SİNDEKİ KÖŞK İLÇESIN' DEN 6.5KM.MESAFEDEKİ MEZEKÖY'DEDİR**

28°3'0" Doğu - 37°54'0" Kuzey

YAĞIŞ ALANI : **96.06 km2** **YAKLAŞIK KOT : 177 m**

GÖZLEM SÜRESİ : **14.09.1962 - 30.09.2006**

ORTALAMA AKIMLAR : **Gözlem süresinde 1.062 m3/sn. (39 Yıllık) 2006 Su yılında 1.202 m3/sn.**

ANLIK EN ÇOK VE EN AZ AKIMLAR:

2006 Su yılında anlık ençok akım	**:**	**24.0**	**m3/sn**	**11.02.2006**
2006 Su yılında anlık enaz akım	**:**	**0.001**	**m3/sn**	**01.10.2005**
Gözlem süresinde anlık ençok akım	**:**	**170.**	**m3/sn**	**15.12.1981**
Gözlem süresinde anlık enaz akım	**:**	**0.000**	**m3/sn**	**01.09.1969**

Akımlar 01 Ekim 2005 'den 30 Eylül 2006' a kadar m3/sn olarak

Gün	Ekim	Kasım	Aralık	Ocak	Şubat	Mart	Nisan	Mayıs	Haziran	Temmuz	Ağustos	Eylül
01	0.001	0.044	0.502	0.910	1.56	3.02	2.80	1.30	0.138	0.502	0.009	0.006
02	0.091	0.044	0.428	0.780	1.56	2.80	2.63	1.17	0.138	0.502	0.009	0.006
03	0.091	0.091	0.428	0.780	1.56	2.80	2.46	1.30	0.138	0.502	0.009	0.006
04	0.044	0.091	0.428	0.650	1.56	2.63	2.46	1.30	0.138	0.650	0.009	0.008
05	0.028	0.091	0.354	0.910	1.56	2.46	2.29	1.30	0.138	0.650	0.009	0.008
06	0.015	0.091	0.354	0.780	2.29	2.46	2.12	0.354	0.138	0.354	0.009	0.006
07	0.009	0.091	0.354	0.910	3.90	3.02	2.12	1.17	0.138	0.280	0.009	0.006
08	0.010	0.138	0.354	0.910	3.68	5.62	1.95	1.17	0.138	0.233	0.009	0.006
09	0.010	0.138	0.354	0.910	3.02	5.10	1.95	1.17	0.138	0.233	0.009	0.006
10	0.009	0.138	0.354	0.780	6.40	4.38	1.82	1.17	0.138	0.233	0.009	0.006
11	0.010	0.138	0.354	0.780	17.9	3.90	1.82	1.17	0.138	0.091	0.009	0.006
12	0.015	0.138	0.354	0.650	14.4	3.90	1.69	0.910	0.138	0.010	0.009	0.005
13	0.015	0.138	0.354	0.650	9.50	6.40	1.69	0.576	0.138	0.010	0.009	0.005
14	0.028	0.138	0.354	0.650	4.86	12.7	1.82	0.576	0.138	0.010	0.009	0.003
15	0.044	0.138	0.354	0.650	5.62	10.2	1.69	0.576	0.138	0.010	0.008	0.003
16	0.044	0.138	0.428	0.576	4.86	8.26	1.56	0.576	0.354	0.010	0.008	0.003
17	0.044	0.138	0.428	0.576	4.38	7.02	1.56	0.576	0.576	0.010	0.008	0.003
18	0.044	0.780	0.502	0.576	4.62	6.71	1.56	0.576	0.576	0.010	0.009	0.001
19	0.091	0.576	0.910	4.38	4.14	5.88	1.43	0.576	0.576	0.010	0.008	0.001
20	0.091	1.04	0.576	5.10	3.90	5.36	1.43	0.576	0.576	0.010	0.008	0.001
21	0.091	0.428	0.502	2.63	3.68	5.10	1.43	0.576	0.576	0.010	0.008	0.001
22	0.091	0.354	0.502	2.12	3.24	4.62	1.43	0.576	0.576	0.010	0.006	0.001
23	0.091	0.428	0.502	1.95	3.02	4.62	1.69	0.576	0.576	0.010	0.006	0.001
24	0.091	0.650	0.428	2.29	2.80	4.38	1.43	0.576	0.576	0.010	0.008	0.001
25	0.044	0.576	0.428	3.90	3.24	4.14	1.30	0.576	0.576	0.009	0.008	0.008
26	0.028	0.428	0.428	3.02	3.24	3.90	1.30	0.576	0.576	0.009	0.006	0.006
27	0.028	0.280	0.428	2.46	3.24	3.68	1.30	0.576	0.576	0.009	0.006	0.006
28	0.028	0.186	0.428	2.12	3.02	3.46	1.30	0.576	0.576	0.009	0.006	0.005
29	0.028	0.091	0.780	1.95	-----	3.24	1.30	0.576	0.576	0.009	0.006	0.003
30	0.044	0.044	0.650	1.82	-----	3.02	1.17	0.576	0.502	0.009	0.006	0.003
31	0.044	-----	1.04	1.69	-----	2.80	-----	0.354	-----	0.009	0.006	-----
Maks.	0.502	1.69	1.69	15.7	24.0	17.9	3.02	7.33	0.576	1.69	0.186	0.008
Min.	0.001	0.044	0.354	0.576	1.56	2.29	1.17	0.354	0.005	0.009	0.006	0.001
Ortalama	0.043	0.259	0.472	1.58	4.53	4.76	1.75	0.781	0.347	0.143	0.008	0.004
LT/SN/Km2	0.451	2.70	4.92	16.4	47.1	49.6	18.2	8.13	3.61	1.49	0.083	0.045
AKIM mm.	1.21	7.00	13.2	43.9	114.	133.	47.2	21.8	9.37	3.98	0.222	0.117
MİL. M3	0.116	0.673	1.26	4.22	11.0	12.8	4.54	2.09	0.900	0.382	0.021	0.011

SU YILI (2006) YILLIK TOPLAM AKIM 38.01 MİLYON M3 396 MM. 12.5 LT/SN/Km2

07. Büyük Menderes Havzasi

D07A032 BÜYÜK MENDERES N. NAZİLLI KÖPRÜSÜ

YERİ : **NAZİLLİ-BOZDOĞAN YOLUNUN 4.KM.DEKİ B. MENDERES NEHRİ ÜZERINDEKI ESKI KÖPRÜDEDİR**

28°19'39" Doğu - 37°52'33" Kuzey

YAĞIŞ ALANI : **14193,00 km2** **YAKLAŞIK KOT : 69 m**

GÖZLEM SÜRESİ : **14.09.1962 - 30.09.2006**

ORTALAMA AKIMLAR : **Gözlem süresinde 40.373 m3/sn. (39 Yıllık) 2006 Su yılında 19.523 m3/sn.**

ANLIK EN ÇOK VE EN AZ AKIMLAR:

2006 Su yılında anlık ençok akım	**:**	**114.**	**m3/sn**	**14.03.2006**
2006 Su yılında anlık enaz akım	**:**	**7.22**	**m3/sn**	**28.10.2005**
Gözlem süresinde anlık ençok akım	**:**	**250.**	**m3/sn**	**17.02.1963**
Gözlem süresinde anlık enaz akım	**:**	**0.503**	**m3/sn**	**19.09.1992**

Akımlar 01 Ekim 2005 'den 30 Eylül 2006' a kadar m3/sn olarak

Gün	Ekim	Kasım	Aralık	Ocak	Şubat	Mart	Nisan	Mayıs	Haziran	Temmuz	Ağustos	Eylül
01	11.8	10.3	16.4	18.0	19.7	23.5	30.6	10.9	8.60	35.0	27.0	21.2
02	16.4	9.32	16.1	17.2	19.0	22.1	30.6	11.9	8.60	31.4	27.4	22.9
03	32.5	10.1	15.8	17.7	19.0	21.7	30.6	15.8	8.60	29.0	27.4	25.0
04	21.0	10.8	15.5	17.7	18.4	21.4	30.6	12.1	8.60	39.4	16.6	25.4
05	16.4	11.1	15.0	18.0	17.7	20.7	30.2	22.9	8.60	56.5	24.3	23.6
06	13.4	10.6	15.3	19.7	21.7	19.7	30.2	18.0	8.60	42.2	25.4	18.4
07	13.4	10.6	15.0	20.7	34.8	19.7	21.2	13.9	8.60	37.8	25.4	16.6
08	13.4	10.3	15.0	18.4	40.5	31.7	15.5	11.9	8.60	37.4	24.0	16.9
09	13.4	10.3	14.7	18.0	30.8	35.7	14.2	11.6	8.80	35.4	23.3	16.9
10	13.4	9.32	14.5	17.2	29.6	27.9	13.9	11.4	15.5	33.8	24.0	16.9
11	13.4	8.60	14.5	16.9	63.4	25.3	13.1	9.80	13.6	32.2	22.9	17.4
12	13.1	8.36	14.2	16.6	72.4	24.5	11.9	9.80	14.9	29.0	18.4	22.6
13	11.3	9.08	13.9	16.4	50.9	32.1	12.1	9.80	15.2	27.8	15.8	20.8
14	9.32	9.08	14.2	16.4	38.5	75.4	10.9	9.80	20.8	30.2	20.5	22.2
15	9.32	9.08	14.5	16.1	32.5	56.0	13.6	9.80	13.4	28.6	19.4	19.1
16	9.32	9.32	15.3	16.4	28.7	44.6	14.2	9.80	10.0	27.8	20.5	18.7
17	9.32	10.1	15.0	16.1	26.8	39.8	11.6	9.80	10.9	26.6	18.4	20.5
18	9.80	13.1	14.5	15.8	27.2	37.4	10.0	9.60	10.2	27.0	18.4	19.4
19	9.80	15.3	47.0	19.0	26.8	37.4	9.60	9.80	9.80	25.4	18.0	15.5
20	9.56	15.8	28.7	33.9	25.3	33.4	9.60	9.80	9.80	23.6	15.8	11.9
21	9.56	16.1	24.9	22.1	24.2	32.6	9.60	9.80	11.2	23.3	16.3	10.9
22	9.56	13.4	22.8	19.0	23.1	31.8	9.40	8.80	15.5	23.6	16.3	10.9
23	9.56	12.8	19.7	18.7	22.4	31.4	9.60	8.60	13.1	23.6	15.2	10.9
24	9.56	12.8	18.7	19.4	21.7	31.0	9.80	8.60	15.2	24.0	12.4	10.9
25	9.56	13.9	18.0	42.0	21.0	31.4	10.7	8.60	20.8	25.8	13.4	16.9
26	9.56	41.5	18.0	29.6	21.0	32.6	9.40	8.60	23.3	25.0	17.4	22.9
27	9.56	24.2	18.4	32.5	22.4	31.0	9.20	8.60	33.4	25.0	16.6	14.4
28	8.36	19.4	18.4	30.8	21.0	31.0	9.60	8.60	37.0	22.9	17.7	12.1
29	7.22	17.2	18.7	26.8	-----	31.0	10.0	8.60	35.8	24.7	19.1	11.2
30	9.56	16.9	18.7	22.1	-----	31.0	12.4	8.60	35.8	25.8	20.8	10.9
31	10.1	-----	18.4	20.3	-----	30.6	-----	8.60	-----	26.6	21.2	-----
Maks.	39.0	59.8	47.0	58.0	81.4	114.	56.5	28.2	43.0	61.6	28.6	27.4
Min.	7.22	7.64	13.9	15.5	17.4	18.4	8.80	8.60	8.60	20.1	10.9	10.9
Ortalama	12.0	13.3	18.1	21.0	29.3	32.1	15.5	10.8	15.4	29.9	20.0	17.5
LT/SN/Km2	0.844	0.937	1.27	1.48	2.06	2.26	1.09	0.760	1.09	2.11	1.41	1.23
AKIM mm.	2.26	2.43	3.41	3.95	4.99	6.06	2.82	2.03	2.82	5.64	3.77	3.19
MİL. M3	32.1	34.5	48.4	56.1	70.9	86.0	40.1	28.9	40.0	80.0	53.5	45.3

SU YILI (2006) YILLIK TOPLAM AKIM 615.80 MİLYON M3 43 MM. 1.4 LT/SN/Km2

07. Büyük Menderes Havzasi

D07A052 GÖMÜ D. ÇEVREPİNAR

YERİ : **SANDIKLI-BANAZ YOLUNUN 27 KM SİNDEKİ ÇEVREPINAR KÖPRÜSÜNDEDİR. HARİTA PAFTA NO: L24-A1**
29°59'17" Doğu - 38°30'9" Kuzey

YAĞIŞ ALANI : **275,60 km2** **YAKLAŞIK KOT : 980 m**

GÖZLEM SÜRESİ : **01.11.1965 - 30.09.2006**

ORTALAMA AKIMLAR : **Gözlem süresinde 0.449 m3/sn. (37 Yıllık) 2006 Su yılında 0.183 m3/sn.**

ANLIK EN ÇOK VE EN AZ AKIMLAR:

2006 Su yılında anlık ençok akım	:	**2.31**	**m3/sn**	**24.03.2006**
2006 Su yılında anlık enaz akım	:	**0.000**	**m3/sn**	**01.10.2005**
Gözlem süresinde anlık ençok akım	:	**52.0**	**m3/sn**	**24.05.1972**
Gözlem süresinde anlık enaz akım	:	**0.000**	**m3/sn**	**16.06.1969**

16. Anahtar Eğrisi (Seviyeler cm olarak)

Seviye	Akım	Seviye	Akım	Seviye	Akım	Seviye	Akım
1	0.000	22	1.1	43	6.2	65	19.0
6	0.006	26	1.7	47	7.6	67	20.8
10	0.100	30	2.4	51	9.4	74	26.5
14	0.320	34	3.3	55	11.5	79	30.5
18	0.640	38	4.4	59	13.5	90	39.0

Akımlar 01 Ekim 2005 'den 30 Eylül 2006' a kadar m3/sn olarak

Gün	Ekim	Kasım	Aralık	Ocak	Şubat	Mart	Nisan	Mayıs	Haziran	Temmuz	Ağustos	Eylül
01	KURU	KURU	KURU	KURU	KURU	0.240	1.48	0.195	KURU	KURU	KURU	KURU
02	KURU	KURU	KURU	KURU	KURU	0.435	1.32	0.195	KURU	KURU	KURU	KURU
03	KURU	KURU	KURU	KURU	KURU	1.15	1.15	0.195	KURU	KURU	KURU	KURU
04	KURU	KURU	KURU	KURU	KURU	1.65	1.15	0.195	KURU	KURU	KURU	KURU
05	KURU	KURU	KURU	KURU	KURU	1.15	1.03	0.195	KURU	KURU	KURU	KURU
06	KURU	KURU	KURU	KURU	KURU	1.15	0.917	0.150	KURU	KURU	KURU	KURU
07	KURU	KURU	KURU	KURU	KURU	1.15	0.800	0.305	KURU	KURU	KURU	KURU
08	KURU	KURU	KURU	KURU	KURU	1.32	0.680	0.240	KURU	KURU	KURU	KURU
09	KURU	KURU	KURU	KURU	KURU	1.32	0.680	0.500	KURU	KURU	KURU	KURU
10	KURU	KURU	KURU	KURU	KURU	0.917	0.680	0.370	KURU	KURU	KURU	KURU
11	KURU	KURU	KURU	KURU	KURU	0.800	0.600	0.305	KURU	KURU	KURU	KURU
12	KURU	KURU	KURU	KURU	KURU	0.800	0.600	0.305	KURU	KURU	KURU	KURU
13	KURU	KURU	KURU	KURU	KURU	1.03	0.600	0.240	KURU	KURU	KURU	KURU
14	KURU	KURU	KURU	KURU	0.500	2.15	0.600	0.195	KURU	KURU	KURU	KURU
15	KURU	KURU	KURU	KURU	0.110	1.65	0.917	0.150	KURU	KURU	KURU	KURU
16	KURU	KURU	KURU	KURU	0.080	1.32	0.600	0.240	KURU	KURU	KURU	KURU
17	KURU	KURU	KURU	KURU	0.110	1.15	0.500	0.240	KURU	KURU	KURU	KURU
18	KURU	KURU	KURU	KURU	0.195	1.03	0.435	0.150	KURU	KURU	KURU	KURU
19	KURU	KURU	KURU	KURU	0.305	0.917	0.435	0.150	KURU	KURU	KURU	KURU
20	KURU	KURU	KURU	KURU	0.305	0.800	0.370	0.150	KURU	KURU	KURU	KURU
21	KURU	KURU	KURU	KURU	0.305	0.917	0.305	0.080	KURU	KURU	KURU	KURU
22	KURU	KURU	KURU	KURU	0.305	1.03	0.305	0.080	KURU	KURU	KURU	KURU
23	KURU	KURU	KURU	KURU	0.370	1.48	0.305	0.016	KURU	KURU	KURU	KURU
24	KURU	KURU	KURU	KURU	0.370	2.31	0.305	0.008	KURU	KURU	KURU	KURU
25	KURU	KURU	KURU	KURU	0.370	2.15	0.305	KURU	KURU	KURU	KURU	KURU
26	KURU	KURU	KURU	KURU	0.370	1.82	0.305	KURU	KURU	KURU	KURU	KURU
27	KURU	KURU	KURU	KURU	0.370	1.65	0.240	KURU	KURU	KURU	KURU	KURU
28	KURU	KURU	KURU	KURU	0.240	1.48	0.195	KURU	KURU	KURU	KURU	KURU
29	KURU	KURU	KURU	KURU	-----	1.32	0.240	KURU	KURU	KURU	KURU	KURU
30	KURU	KURU	KURU	KURU	-----	1.32	0.240	KURU	KURU	KURU	KURU	KURU
31	KURU	-----	KURU	KURU	-----	1.82	-----	KURU	-----	KURU	KURU	-----
Maks.	KURU	KURU	KURU	KURU	0.500	2.31	1.48	0.500	KURU	KURU	KURU	KURU
Min.	KURU	KURU	KURU	KURU	KURU	0.240	0.195	KURU	KURU	KURU	KURU	KURU
Ortalama	KURU	KURU	KURU	KURU	0.154	1.27	0.610	0.156	KURU	KURU	KURU	KURU
LT/SN/Km2	0.000	0.000	0.000	0.000	0.558	4.61	2.21	0.568	0.000	0.000	0.000	0.000
AKIM mm.	0.000	0.000	0.000	0.000	1.35	12.4	5.73	1.52	0.000	0.000	0.000	0.000
MİL. M3	0.000	0.000	0.000	0.000	0.372	3.41	1.58	0.419	0.000	0.000	0.000	0.000

SU YILI (2006) YILLIK TOPLAM AKIM 5.78 MİLYON M3 21 MM. 0.7 LT/SN/Km2

07. Büyük Menderes Havzasi

D07A059 ÇÜRÜKSU YUKARI ŞAMLI

YERİ : **DENİZLİ-SARAYKÖY YOLUNUN 13.5 KM.DEN SAĞA AYRILAN YOLUN 8.KMDEKİ YK.ŞAMLI KÖYÜNDEDİR**

29°4'0" Doğu - 37°55'0" Kuzey

YAĞIŞ ALANI : **1726,00 km2** **YAKLAŞIK KOT : 160 m**

GÖZLEM SÜRESİ : **05.01.1968 - 30.09.2006**

ORTALAMA AKIMLAR : **Gözlem süresinde 8.436 m3/sn. (31 Yıllık) 2006 Su yılında 7.213 m3/sn.**

ANLIK EN ÇOK VE EN AZ AKIMLAR:

2006 Su yılında anlık ençok akım	**:**	**24.0**	**m3/sn**	**02.10.2005**
2006 Su yılında anlık enaz akım	**:**	**0.523**	**m3/sn**	**04.09.2006**
Gözlem süresinde anlık ençok akım	**:**	**84.0**	**m3/sn**	**28.02.1973**
Gözlem süresinde anlık enaz akım	**:**	**0.000**	**m3/sn**	**02.06.1984**

Akımlar 01 Ekim 2005 'den 30 Eylül 2006' a kadar m3/sn olarak

Gün	Ekim	Kasım	Aralık	Ocak	Şubat	Mart	Nisan	Mayıs	Haziran	Temmuz	Ağustos	Eylül
01	7.70	11.5	14.2	13.5	10.2	10.2	8.20	3.18	1.78	2.56	1.48	1.40
02	14.1	12.2	14.3	14.5	10.3	10.0	7.70	3.50	1.85	2.42	1.55	1.40
03	12.1	13.4	14.2	14.2	10.3	10.0	7.30	3.02	1.78	2.28	1.78	1.40
04	11.6	13.8	14.1	12.6	10.3	10.1	7.10	4.06	1.78	2.21	1.70	1.33
05	11.3	13.2	14.1	13.5	10.3	9.90	6.82	6.28	1.78	5.11	1.70	1.08
06	11.4	13.1	14.1	14.2	10.3	9.70	6.28	4.66	1.78	3.26	1.63	1.40
07	11.4	13.3	13.9	12.7	10.3	9.50	5.74	5.20	1.85	2.63	1.63	1.40
08	11.6	13.8	13.7	12.8	10.3	11.2	5.56	4.14	1.63	2.28	1.63	1.08
09	11.3	12.7	13.7	12.4	10.3	10.4	5.47	3.34	1.33	1.55	1.70	1.02
10	11.3	12.0	13.9	12.2	10.3	9.50	5.47	3.02	1.25	1.48	1.70	1.19
11	11.4	12.2	13.8	12.2	10.3	9.40	5.20	2.63	1.19	1.48	1.78	1.70
12	11.0	13.7	13.7	12.1	10.3	9.30	4.57	2.07	1.19	1.48	1.85	1.40
13	10.9	13.7	13.8	12.0	10.3	10.5	4.14	2.07	1.40	1.55	1.85	1.33
14	10.7	13.6	14.0	12.0	10.3	11.7	4.57	2.07	2.07	1.78	1.85	1.25
15	10.6	13.9	14.4	12.0	10.4	10.3	5.11	2.00	2.00	1.70	2.35	1.33
16	11.3	14.0	14.2	12.1	10.5	9.80	4.39	2.00	2.28	1.70	2.28	1.25
17	12.0	14.0	14.0	12.2	10.4	9.50	3.42	2.07	2.28	1.70	2.21	1.33
18	12.3	16.7	14.6	12.3	10.4	9.60	2.94	2.00	1.63	1.70	3.02	1.40
19	12.7	14.5	17.9	12.4	10.2	9.20	2.86	2.00	1.55	1.70	2.35	1.55
20	12.8	17.1	14.7	13.4	10.1	9.10	1.93	2.00	1.55	1.70	2.28	1.33
21	12.8	14.7	14.6	12.3	10.2	9.20	1.70	2.00	1.70	1.70	2.14	1.55
22	12.4	14.4	14.1	12.3	10.3	9.20	1.70	1.93	2.14	1.70	2.07	2.42
23	11.7	14.3	14.0	12.5	9.90	9.20	1.85	1.55	2.14	1.70	2.00	3.66
24	11.1	14.4	13.9	12.9	9.80	9.50	2.28	1.40	2.21	1.78	1.93	3.58
25	11.1	14.3	13.6	14.1	9.90	10.4	2.00	1.48	2.21	1.70	1.93	4.48
26	11.1	16.5	13.7	12.9	10.0	9.30	2.14	1.55	3.18	1.70	1.78	3.98
27	11.0	14.5	12.9	10.5	9.90	9.00	2.49	1.55	5.47	1.70	1.78	3.82
28	11.2	14.1	13.9	10.2	10.2	9.00	2.94	1.55	3.26	1.55	1.70	3.98
29	11.4	14.3	14.2	10.1	-----	8.90	3.18	1.55	3.02	1.63	1.70	3.98
30	11.4	14.2	14.1	10.0	-----	8.80	2.94	1.55	2.78	1.70	1.70	3.98
31	11.5	-----	13.9	10.1	-----	8.90	-----	1.70	-----	1.40	1.70	-----
Maks.	24.0	23.4	22.7	18.4	12.6	15.2	9.20	11.3	13.1	9.50	7.00	10.4
Min.	7.30	11.2	12.7	9.50	9.40	8.40	0.554	0.851	1.02	1.08	1.33	0.523
Ortalama	11.5	13.9	14.1	12.4	10.2	9.69	4.27	2.55	2.07	1.95	1.90	2.07
LT/SN/Km2	6.66	8.07	8.19	7.16	5.92	5.61	2.47	1.48	1.20	1.13	1.10	1.20
AKIM mm.	17.8	20.9	21.9	19.2	14.3	15.0	6.41	3.96	3.11	3.03	2.94	3.10
MİL. M3	30.8	36.1	37.9	33.1	24.7	25.9	11.1	6.84	5.36	5.23	5.08	5.36

SU YILI (2006) YILLIK TOPLAM AKIM 227.47 MİLYON M3 132 MM. 4.2 LT/SN/Km2

07. Büyük Menderes Havzasi

D07A061 DANDALAS ÇAYI . BEŞDEĞİRMENLER

YERİ : **AYDIN İLİ KUYUCAK-KARACASU YOLUNUN 31.KM. DEKİ YENİCE NAHİYESİ BEŞDEĞİRMENLER MEVKİSİNDEDİR**

28°34'48" Doğu - 37°48'18" Kuzey

YAĞIŞ ALANI : **589,80 km2** **YAKLAŞIK KOT : 199 m**

GÖZLEM SÜRESİ : **16.01.1968 - 30.09.2006**

ORTALAMA AKIMLAR : **Gözlem süresinde 2.198 m3/sn. (26 Yıllık) 2006 Su yılında 1.915 m3/sn.**

ANLIK EN ÇOK VE EN AZ AKIMLAR:

2006 Su yılında anlık ençok akım	**:**	**31.8**	**m3/sn**	**19.12.2005**
2006 Su yılında anlık enaz akım	**:**	**0.015**	**m3/sn**	**04.08.2006**
Gözlem süresinde anlık ençok akım	**:**	**250.**	**m3/sn**	**11.02.1984**
Gözlem süresinde anlık enaz akım	**:**	**0.001**	**m3/sn**	**01.10.2001**

14. Anahtar Eğrisi (Seviyeler cm olarak)

Seviye	Akım	Seviye	Akım	Seviye	Akım	Seviye	Akım
10	0.013	16	0.077	26	0.465	45	2.8
11	0.018	17	0.111	29	0.669	51	3.9
12	0.026	19	0.159	32	0.956	57	5.6
13	0.038	21	0.229	36	1.4	65	8.0
14	0.054	23	0.326	40	1.9	97	21.1

Akımlar 01 Ekim 2005 'den 30 Eylül 2006' a kadar m3/sn olarak

Gün	Ekim	Kasım	Aralık	Ocak	Şubat	Mart	Nisan	Mayıs	Haziran	Temmuz	Ağustos	Eylül
01	0.421	1.28	6.10	6.10	0.812	1.51	1.77	1.03	0.533	1.64	0.118	0.092
02	0.421	1.28	5.89	6.10	0.812	1.28	1.64	1.03	0.533	1.50	0.092	0.092
03	0.646	1.28	5.89	6.10	0.812	1.28	1.50	0.919	0.533	1.64	0.092	0.092
04	0.894	1.40	5.89	6.30	0.812	1.28	1.77	1.50	0.465	2.20	0.027	0.172
05	1.17	1.40	5.89	3.54	0.812	1.17	2.04	2.04	0.465	1.91	0.065	0.289
06	1.40	1.40	6.10	1.62	2.04	1.17	1.64	1.77	0.406	1.37	0.092	0.231
07	1.62	1.40	6.10	1.51	2.82	1.28	1.50	1.64	0.348	1.03	0.092	0.231
08	1.76	1.40	6.10	1.62	2.49	6.26	1.37	1.37	0.406	0.738	0.092	0.038
09	1.90	1.40	6.10	1.62	2.49	4.15	1.37	1.26	0.406	0.670	0.092	0.027
10	1.90	1.40	6.10	2.04	2.49	2.68	1.37	1.37	0.465	0.601	0.172	0.027
11	1.90	1.40	6.30	2.18	2.49	2.36	1.37	0.806	0.601	0.601	0.172	0.065
12	1.90	1.40	6.30	2.18	2.49	2.36	1.26	0.738	0.533	0.406	0.145	0.038
13	1.76	1.40	6.30	2.18	2.49	2.36	1.26	0.738	0.670	0.231	0.118	0.065
14	1.76	1.40	6.30	2.18	2.18	2.36	1.91	0.533	2.52	0.231	0.118	0.092
15	1.76	1.40	6.30	2.18	1.90	2.36	2.36	0.533	0.919	0.231	0.118	0.118
16	1.76	1.51	6.10	2.18	1.90	2.36	1.64	0.533	0.919	0.231	0.118	0.118
17	1.76	1.62	6.10	2.18	1.90	2.36	1.37	0.533	0.806	0.231	0.038	0.092
18	1.62	2.04	6.50	2.18	1.90	2.36	1.37	0.465	0.533	0.231	0.038	0.118
19	1.51	1.51	17.9	2.49	1.90	2.36	1.26	0.465	0.533	0.231	0.118	0.092
20	1.51	1.40	14.7	2.98	1.90	2.68	1.26	0.533	0.533	0.231	0.118	0.145
21	1.17	1.40	14.7	1.76	1.90	2.84	1.14	0.533	0.601	0.289	0.092	0.172
22	0.812	1.40	14.7	1.76	1.90	2.52	1.26	0.465	1.50	0.289	0.065	0.172
23	0.812	1.51	14.7	1.76	1.62	2.52	1.37	0.465	1.37	0.231	0.065	0.231
24	0.812	1.62	14.7	3.15	1.76	2.36	1.26	0.465	1.26	0.231	0.027	0.601
25	0.812	1.17	14.7	8.70	1.90	2.36	1.14	0.465	1.26	0.231	0.038	1.03
26	0.977	6.30	11.3	2.98	1.90	2.20	1.14	0.465	1.37	0.145	0.065	0.670
27	1.06	6.10	6.10	2.18	1.90	2.04	1.14	0.465	2.68	0.172	0.092	0.601
28	1.06	6.10	6.10	0.977	1.62	1.91	1.03	0.465	2.04	0.145	0.092	0.601
29	1.17	6.10	6.50	0.894	-----	1.91	1.14	0.465	1.77	0.145	0.289	0.670
30	1.28	6.10	6.30	0.812	-----	1.77	1.03	0.533	1.64	0.145	0.231	0.670
31	1.28	-----	6.10	0.812	-----	1.77	-----	0.465	-----	0.118	0.145	-----
Maks.	11.5	11.3	31.8	16.8	11.3	8.02	3.41	3.22	16.0	4.52	0.533	2.68
Min.	0.421	0.894	4.31	0.729	0.812	1.17	1.03	0.406	0.348	0.118	0.015	0.027
Ortalama	1.31	2.22	8.35	2.75	1.85	2.26	1.42	0.808	0.954	0.590	0.104	0.255
LT/SN/Km2	2.22	3.76	14.2	4.66	3.15	3.84	2.41	1.37	1.62	1.00	0.177	0.432
AKIM mm.	5.95	9.74	37.9	12.5	7.61	10.3	6.25	3.67	4.19	2.68	0.474	1.12
MİL. M3	3.51	5.75	22.4	7.37	4.49	6.06	3.69	2.16	2.47	1.58	0.280	0.661

SU YILI (2006) YILLIK TOPLAM AKIM 60.42 MİLYON M3 102 MM. 3.2 LT/SN/Km2

07. Büyük Menderes Havzasi

D07A065 BÜYÜK MENDERES N. ADIGÜZEL

YERİ : **GÜNEY'E 21.KM.MESAFEDEKİ ADIGÜZEL BARAJI'NIN 2KM.MANSABINDADIR.**
29°12'0" Doğu - 38°9'0" Kuzey

YAĞIŞ ALANI : **9006,00 km2** **YAKLAŞIK KOT : 307 m**

GÖZLEM SÜRESİ : **15.01.1968 - 30.09.2006**

ORTALAMA AKIMLAR : **Gözlem süresinde 23.602 m3/sn. (33 Yıllık) 2006 Su yılında 16.953 m3/sn.**

ANLIK EN ÇOK VE EN AZ AKIMLAR:

2006 Su yılında anlık ençok akım	:	**66.9**	**m3/sn**	**16.07.2006**
2006 Su yılında anlık enaz akım	:	**0.000**	**m3/sn**	**02.10.2005**
Gözlem süresinde anlık ençok akım	:	**500.**	**m3/sn**	**11.02.1984**
Gözlem süresinde anlık enaz akım	:	**0.000**	**m3/sn**	**19.12.1989**

Akımlar 01 Ekim 2005 'den 30 Eylül 2006' a kadar m3/sn olarak

Gün	Ekim	Kasım	Aralık	Ocak	Şubat	Mart	Nisan	Mayıs	Haziran	Temmuz	Ağustos	Eylül
01	10.4	KURU	KURU	KURU	KURU	KURU	KURU	22.5	20.0	63.2	63.2	56.6
02	KURU	KURU	KURU	KURU	KURU	KURU	KURU	20.0	17.9	66.9	60.3	56.6
03	KURU	KURU	KURU	KURU	KURU	KURU	KURU	17.9	18.7	66.9	50.1	55.4
04	KURU	KURU	KURU	KURU	KURU	KURU	KURU	0.128	19.5	64.7	62.5	56.0
05	KURU	KURU	KURU	KURU	KURU	KURU	KURU	KURU	20.5	47.0	62.5	56.0
06	KURU	KURU	KURU	KURU	KURU	KURU	KURU	KURU	22.5	50.1	62.5	50.1
07	KURU	KURU	KURU	KURU	KURU	KURU	KURU	KURU	27.8	58.1	61.8	43.8
08	KURU	KURU	KURU	KURU	KURU	KURU	KURU	KURU	28.9	58.8	61.8	43.1
09	KURU	KURU	KURU	KURU	KURU	KURU	KURU	8.05	36.6	58.8	61.8	43.1
10	KURU	KURU	KURU	KURU	KURU	KURU	KURU	11.8	33.7	58.8	58.8	43.1
11	KURU	KURU	KURU	KURU	KURU	KURU	KURU	11.8	33.7	59.6	55.4	43.1
12	KURU	KURU	KURU	KURU	KURU	KURU	KURU	12.1	33.7	59.6	54.8	43.1
13	KURU	KURU	KURU	KURU	KURU	KURU	KURU	11.8	32.1	59.6	54.8	40.5
14	KURU	KURU	KURU	KURU	KURU	KURU	KURU	11.8	15.7	60.3	54.8	32.1
15	KURU	KURU	KURU	KURU	KURU	KURU	KURU	11.8	14.8	59.6	54.8	31.5
16	KURU	KURU	KURU	KURU	KURU	KURU	KURU	11.8	21.0	59.6	54.8	31.5
17	KURU	KURU	KURU	KURU	KURU	KURU	KURU	11.8	21.5	59.6	54.2	31.5
18	KURU	KURU	KURU	KURU	KURU	KURU	KURU	11.8	21.5	59.6	53.6	28.3
19	KURU	KURU	KURU	KURU	KURU	KURU	KURU	11.8	25.8	61.0	53.6	22.5
20	KURU	KURU	KURU	KURU	KURU	KURU	8.80	11.8	37.3	61.8	53.0	19.1
21	KURU	KURU	KURU	KURU	KURU	KURU	13.2	11.8	45.1	61.8	52.4	14.4
22	KURU	KURU	KURU	KURU	KURU	KURU	17.9	11.8	51.3	61.8	43.8	10.0
23	KURU	KURU	KURU	KURU	KURU	KURU	18.3	11.8	53.6	61.8	43.1	10.0
24	KURU	KURU	KURU	KURU	KURU	KURU	18.3	12.1	58.8	61.8	48.3	10.0
25	KURU	KURU	KURU	0.875	KURU	KURU	18.3	12.8	58.8	63.2	53.0	KURU
26	KURU	KURU	KURU	24.8	KURU	KURU	21.0	19.1	58.8	63.2	53.0	KURU
27	KURU	KURU	KURU	KURU	KURU	KURU	23.9	19.5	58.8	63.2	53.0	KURU
28	KURU	KURU	KURU	KURU	KURU	KURU	23.9	19.5	58.8	63.2	55.4	KURU
29	6.80	KURU	KURU	KURU	-----	KURU	23.9	19.5	58.8	63.2	57.3	KURU
30	9.65	KURU	KURU	KURU	-----	KURU	23.9	19.5	58.8	63.2	57.3	KURU
31	6.80	-----	KURU	KURU	-----	KURU	-----	19.5	-----	63.2	56.6	-----
Maks.	10.4	KURU	KURU	32.6	KURU	KURU	23.9	22.5	58.8	66.9	63.2	56.6
Min.	KURU	KURU	KURU	KURU	KURU	KURU	KURU	KURU	14.4	44.4	33.7	KURU
Ortalama	1.09	KURU	KURU	0.828	KURU	KURU	7.05	12.1	35.5	60.7	55.6	29.0
LT/SN/Km2	0.121	0.000	0.000	0.092	0.000	0.000	0.782	1.35	3.94	6.75	6.17	3.23
AKIM mm.	0.323	0.000	0.000	0.246	0.000	0.000	2.03	3.60	10.2	18.1	16.5	8.36
MİL. M3	2.91	0.000	0.000	2.22	0.000	0.000	18.3	32.4	92.0	163.	149.	75.3

SU YILI (2006) YILLIK TOPLAM AKIM 535.13 MİLYON M3 59 MM. 1.9 LT/SN/Km2

07. Büyük Menderes Havzasi

D07A071 BÜYÜK MENDERES N. YUKARI SEYİTLER

YERİ : **ÇAL-DENİZLİ YOLUNUN 5.5 KM.DE YK.SEYİT KÖPRÜSÜNÜN 500 M.MANSABINDADIR.**
29°26'0" Doğu - 38°3'0" Kuzey

YAĞIŞ ALANI : **4203,00 km2** **YAKLAŞIK KOT : 758 m**

GÖZLEM SÜRESİ : **15.05.1969 - 30.09.2006**

ORTALAMA AKIMLAR : **Gözlem süresinde 10.033 m3/sn. (35 Yıllık) 2006 Su yılında 2.823 m3/sn.**

ANLIK EN ÇOK VE EN AZ AKIMLAR:

2006 Su yılında anlık ençok akım	:	**7.96**	**m3/sn**	**29.03.2006**
2006 Su yılında anlık enaz akım	:	**1.91**	**m3/sn**	**08.10.2005**
Gözlem süresinde anlık ençok akım	:	**44.0**	**m3/sn**	**19.08.1981**
Gözlem süresinde anlık enaz akım	:	**0.041**	**m3/sn**	**01.10.1993**

Akımlar 01 Ekim 2005 'den 30 Eylül 2006' a kadar m3/sn olarak

Gün	Ekim	Kasım	Aralık	Ocak	Şubat	Mart	Nisan	Mayıs	Haziran	Temmuz	Ağustos	Eylül
01	2.45	2.00	2.30	2.15	2.15	2.45	3.50	2.75	2.30	4.25	3.95	2.45
02	2.45	2.00	2.15	2.15	2.15	2.45	3.35	2.75	2.00	4.10	3.95	2.45
03	2.45	2.00	2.15	2.15	2.15	2.45	3.35	2.75	1.91	3.95	3.95	2.30
04	2.45	2.00	2.15	2.15	2.15	2.45	3.35	2.75	2.30	4.10	3.95	2.30
05	2.15	2.00	2.15	2.15	2.15	2.45	3.35	2.90	2.30	4.40	4.25	2.30
06	2.15	2.00	2.15	2.30	2.15	2.45	3.35	2.75	2.30	4.70	4.25	2.30
07	2.00	2.00	2.15	2.45	2.30	2.45	3.35	2.75	2.60	4.25	3.95	2.75
08	1.91	2.00	2.15	2.30	2.30	2.60	3.35	2.90	2.75	3.95	3.80	3.20
09	1.91	2.00	2.15	2.30	2.30	2.60	3.35	2.75	3.20	3.80	3.65	3.80
10	1.91	2.00	2.00	2.30	2.45	2.75	3.35	2.60	3.35	3.95	3.65	3.95
11	1.91	2.00	2.00	2.30	2.45	2.60	3.35	2.60	3.50	3.95	3.65	4.10
12	2.00	2.00	2.00	2.30	2.45	2.60	3.35	2.60	3.50	3.80	3.95	4.25
13	2.00	1.91	2.00	2.30	2.45	2.75	3.05	2.60	3.65	3.65	3.95	4.40
14	2.00	1.91	2.00	2.30	2.60	2.75	2.90	2.60	3.80	4.55	3.95	4.25
15	1.91	1.91	2.00	2.30	2.45	2.90	3.05	2.60	3.80	5.80	3.80	3.80
16	1.91	1.91	2.15	2.30	2.45	2.90	3.05	2.60	3.35	4.85	3.65	3.65
17	1.91	2.15	2.15	2.30	2.45	2.90	3.05	2.60	2.60	4.85	3.65	3.65
18	1.91	2.60	2.15	2.30	2.45	2.90	2.90	2.75	2.60	4.70	3.65	4.10
19	1.91	2.45	2.45	2.30	2.45	2.90	2.75	2.60	2.60	4.10	4.10	4.55
20	1.91	2.45	2.60	2.30	2.45	3.05	2.75	2.60	2.75	3.95	3.65	3.95
21	1.91	2.30	2.45	2.30	2.45	3.05	2.75	2.45	2.60	3.95	3.35	3.05
22	2.00	2.30	4.25	2.30	2.45	3.05	2.60	2.30	3.35	4.10	3.35	2.90
23	3.50	2.15	2.45	2.30	2.45	3.05	2.75	2.30	3.65	3.95	3.05	2.60
24	2.30	2.15	2.30	2.30	2.45	3.05	2.75	2.30	3.65	4.10	2.90	2.60
25	2.15	2.15	2.15	2.45	2.30	3.05	2.90	2.30	3.65	4.25	2.90	2.60
26	2.15	2.15	2.15	2.45	2.30	3.05	2.75	2.30	3.95	4.25	3.35	2.60
27	2.15	2.30	2.15	2.30	2.45	3.05	2.60	2.30	3.80	4.25	3.65	2.60
28	2.00	2.15	2.15	2.15	2.45	3.05	2.60	2.30	3.95	4.25	4.10	2.60
29	2.00	2.15	2.15	2.00	-----	5.00	2.60	2.30	3.95	4.85	3.65	2.45
30	2.00	2.15	2.15	2.00	-----	3.65	2.75	2.30	3.95	4.85	3.35	2.30
31	2.00	-----	2.15	2.15	-----	3.50	-----	2.30	-----	4.85	3.20	-----
Maks.	4.25	2.60	5.00	2.60	2.60	7.96	3.80	3.05	4.40	7.72	4.40	4.55
Min.	1.91	1.91	1.91	2.00	1.91	2.45	2.00	2.30	1.91	3.50	2.90	2.30
Ortalama	2.11	2.11	2.24	2.26	2.36	2.90	3.03	2.56	3.12	4.30	3.68	3.16
LT/SN/Km2	0.502	0.502	0.533	0.538	0.563	0.690	0.721	0.608	0.743	1.02	0.876	0.752
AKIM mm.	1.34	1.30	1.43	1.44	1.36	1.85	1.87	1.63	1.93	2.74	2.35	1.95
MİL. M3	5.65	5.46	6.00	6.06	5.72	7.77	7.85	6.85	8.09	11.5	9.87	8.19

SU YILI (2006) YILLIK TOPLAM AKIM 89.01 MİLYON M3 21 MM. 0.7 LT/SN/Km2

07. Büyük Menderes Havzasi

D07A075 KUMALAR Ç. KARAKUYU

YERİ : **AFYON-ISPARTA YOLUNUN DİNAR YOL KAVŞAGINDAN 2 KM SONRAKİ KÖPRÜNÜN MENBABINDADIR**
HARİTA PAFTA NO: L24-D3
30°12'1" Doğu - 38°7'5" Kuzey

YAĞIŞ ALANI : **230,20 km2** **YAKLAŞIK KOT : 1018 m**

GÖZLEM SÜRESİ : **01.10.1976 - 30.09.2006**

ORTALAMA AKIMLAR : **Gözlem süresinde 0.255 m3/sn. (25 Yıllık) 2006 Su yılında 0.073 m3/sn.**

ANLIK EN ÇOK VE EN AZ AKIMLAR:

2006 Su yılında anlık ençok akım	:	**1.00**	**m3/sn**	**02.03.2006**
2006 Su yılında anlık enaz akım	:	**0.000**	**m3/sn**	**01.10.2005**
Gözlem süresinde anlık ençok akım	:	**19.0**	**m3/sn**	**14.05.1984**
Gözlem süresinde anlık enaz akım	:	**0.000**	**m3/sn**	**01.10.1976**

4. Anahtar Eğrisi (Seviyeler cm olarak)

Seviye	Akım	Seviye	Akım	Seviye	Akım	Seviye	Akım
1	0.000	11	0.180	16	0.500	21	0.940
3	0.000	12	0.235	17	0.575	26	1.4
5	0.009	13	0.290	18	0.660	31	2.0
7	0.039	14	0.360	19	0.740	36	2.6
9	0.086	15	0.420	20	0.840	41	3.3

Akımlar 01 Ekim 2005 'den 30 Eylül 2006' a kadar m3/sn olarak

Gün	Ekim	Kasım	Aralık	Ocak	Şubat	Mart	Nisan	Mayıs	Haziran	Temmuz	Ağustos	Eylül
01	KURU	KURU	KURU	KURU	KURU	0.006	0.320	KURU	KURU	KURU	KURU	KURU
02	KURU	KURU	KURU	KURU	KURU	0.820	0.398	0.210	KURU	KURU	KURU	KURU
03	KURU	KURU	KURU	KURU	KURU	0.632	0.398	0.160	KURU	KURU	KURU	KURU
04	KURU	KURU	KURU	KURU	KURU	0.710	0.260	0.160	KURU	KURU	KURU	KURU
05	KURU	KURU	KURU	KURU	KURU	0.710	0.320	0.160	KURU	KURU	KURU	KURU
06	KURU	KURU	KURU	KURU	KURU	0.710	0.320	0.160	KURU	KURU	KURU	KURU
07	KURU	KURU	KURU	KURU	KURU	0.554	0.320	0.130	KURU	KURU	KURU	KURU
08	KURU	KURU	KURU	KURU	KURU	0.554	0.320	0.130	KURU	KURU	KURU	KURU
09	KURU	KURU	KURU	KURU	KURU	0.554	0.260	0.130	KURU	KURU	KURU	KURU
10	KURU	KURU	KURU	KURU	KURU	0.476	0.320	0.130	KURU	KURU	KURU	KURU
11	KURU	KURU	KURU	KURU	0.210	0.476	0.632	0.080	KURU	KURU	KURU	KURU
12	KURU	KURU	KURU	KURU	0.130	0.476	0.398	0.080	KURU	KURU	KURU	KURU
13	KURU	KURU	KURU	KURU	0.060	0.476	0.260	0.080	KURU	KURU	KURU	KURU
14	KURU	KURU	KURU	KURU	0.024	0.632	0.260	0.080	KURU	KURU	KURU	KURU
15	KURU	KURU	KURU	KURU	KURU	0.632	0.160	0.040	KURU	KURU	KURU	KURU
16	KURU	KURU	KURU	KURU	KURU	0.476	0.160	0.040	KURU	KURU	KURU	KURU
17	KURU	KURU	KURU	KURU	KURU	0.476	0.080	0.013	KURU	KURU	KURU	KURU
18	KURU	KURU	KURU	KURU	KURU	0.476	0.040	KURU	KURU	KURU	KURU	KURU
19	KURU	KURU	KURU	KURU	KURU	0.632	KURU	KURU	KURU	KURU	KURU	KURU
20	KURU	KURU	KURU	KURU	KURU	0.632	KURU	KURU	KURU	KURU	KURU	KURU
21	KURU	KURU	KURU	KURU	KURU	0.632	KURU	KURU	KURU	KURU	KURU	KURU
22	KURU	KURU	KURU	KURU	KURU	0.554	0.002	KURU	KURU	KURU	KURU	KURU
23	KURU	KURU	KURU	KURU	KURU	0.820	0.398	KURU	KURU	KURU	KURU	KURU
24	KURU	KURU	KURU	KURU	KURU	0.910	0.260	KURU	KURU	KURU	KURU	KURU
25	KURU	KURU	KURU	KURU	KURU	0.820	0.160	KURU	KURU	KURU	KURU	KURU
26	KURU	KURU	KURU	KURU	KURU	0.820	0.040	KURU	KURU	KURU	KURU	KURU
27	KURU	KURU	KURU	KURU	KURU	0.710	KURU	KURU	KURU	KURU	KURU	KURU
28	KURU	KURU	KURU	KURU	KURU	0.554	0.024	KURU	KURU	KURU	KURU	KURU
29	KURU	KURU	KURU	KURU	-----	0.554	KURU	KURU	KURU	KURU	KURU	KURU
30	KURU	KURU	KURU	KURU	-----	0.398	KURU	KURU	KURU	KURU	KURU	KURU
31	KURU	-----	KURU	KURU	-----	0.398	-----	KURU	-----	KURU	KURU	-----
Maks.	KURU	KURU	KURU	KURU	0.260	1.00	0.710	0.260	KURU	KURU	KURU	KURU
Min.	KURU	KURU	KURU	KURU	KURU	KURU	KURU	KURU	KURU	KURU	KURU	KURU
Ortalama	KURU	KURU	KURU	KURU	0.015	0.590	0.204	0.058	KURU	KURU	KURU	KURU
LT/SN/Km2	0.000	0.000	0.000	0.000	0.066	2.56	0.885	0.250	0.000	0.000	0.000	0.000
AKIM mm.	0.000	0.000	0.000	0.000	0.159	6.86	2.29	0.669	0.000	0.000	0.000	0.000
MİL. M3	0.000	0.000	0.000	0.000	0.037	1.58	0.528	0.154	0.000	0.000	0.000	0.000

SU YILI (2006) YILLIK TOPLAM AKIM 2.30 MİLYON M3 10 MM. 0.3 LT/SN/Km2

07. Büyük Menderes Havzasi

D07A079 GİRME D. GİRME

YERİ : **YATAGAN-MUĞLA YOLUNUN 5.KM.SİNDEKİ BOZHÜYÜK KÖYÜ YOL AYRIMINDAN 4.5 KM.DEN SONRA GİRME DERESİ KÖPRÜSÜNDEDİR.**
28°6'35" Doğu - 37°17'26" Kuzey

YAĞIŞ ALANI : **123,00 km2** **YAKLAŞIK KOT : 365 m**

GÖZLEM SÜRESİ : **17.06.1980 - 30.09.2006**

ORTALAMA AKIMLAR : **Gözlem süresinde 0.728 m3/sn. (18 Yıllık) 2006 Su yılında 0.496 m3/sn.**

ANLIK EN ÇOK VE EN AZ AKIMLAR:

2006 Su yılında anlık ençok akım	:	**117.**	**m3/sn**	**02.10.2005**
2006 Su yılında anlık enaz akım	:	**0.001**	**m3/sn**	**07.10.2005**
Gözlem süresinde anlık ençok akım	:	**117.**	**m3/sn**	**02.10.2005**
Gözlem süresinde anlık enaz akım	:	**0.000**	**m3/sn**	**31.07.1985**

Akımlar 01 Ekim 2005 'den 30 Eylül 2006' a kadar m3/sn olarak

Gün	Ekim	Kasım	Aralık	Ocak	Şubat	Mart	Nisan	Mayıs	Haziran	Temmuz	Ağustos	Eylül
01	0.176	0.025	0.177	0.662	0.605	2.12	0.549	0.398	0.283	0.360	0.038	0.147
02	4.30	0.031	0.177	0.662	0.549	1.00	0.549	0.398	0.283	0.283	0.038	0.147
03	0.774	0.038	0.177	0.662	0.549	0.887	0.549	0.360	0.283	0.283	0.038	0.147
04	0.436	0.038	0.177	0.605	0.549	0.831	0.549	0.398	0.283	0.360	0.077	0.147
05	0.283	0.038	0.177	0.944	0.492	0.831	0.492	0.398	0.283	0.283	0.129	0.147
06	0.177	0.058	0.147	0.944	0.887	0.831	0.492	0.398	0.283	0.177	0.129	0.147
07	0.094	0.077	0.147	0.774	1.81	1.63	0.436	0.398	0.245	0.177	0.129	0.147
08	0.008	0.077	0.147	0.774	2.23	5.46	0.436	0.398	0.245	0.177	0.129	0.111
09	0.008	0.077	0.147	0.718	1.00	3.23	0.436	0.398	0.245	0.177	0.129	0.077
10	0.011	0.058	0.147	0.718	1.18	1.63	0.436	0.398	0.245	0.177	0.129	0.077
11	0.015	0.058	0.147	0.718	2.78	1.36	0.436	0.360	0.245	0.177	0.177	0.077
12	0.015	0.058	0.177	0.662	2.34	1.45	0.398	0.360	0.245	0.177	0.207	0.077
13	0.015	0.058	0.177	0.662	1.27	6.05	0.398	0.360	0.245	0.177	0.207	0.077
14	0.015	0.058	0.177	0.662	1.00	5.31	0.436	0.360	0.245	0.147	0.177	0.077
15	0.011	0.077	0.549	0.662	0.944	1.72	0.492	0.360	0.245	0.147	0.177	0.077
16	0.015	0.094	0.245	0.662	0.887	1.27	0.436	0.322	0.245	0.147	0.177	0.077
17	0.015	0.129	0.245	0.662	0.887	1.09	0.436	0.322	0.245	0.147	0.207	0.077
18	0.015	0.283	1.81	0.662	0.887	0.944	0.436	0.322	0.245	0.147	0.177	0.077
19	0.015	0.031	7.29	0.662	0.831	0.887	0.398	0.322	0.245	0.147	0.177	0.058
20	0.015	0.129	1.18	0.718	0.831	0.831	0.398	0.322	0.283	0.147	0.177	0.038
21	0.015	0.025	0.944	0.662	0.831	0.831	0.398	0.322	0.322	0.147	0.177	0.038
22	0.015	0.015	0.831	0.662	0.774	0.718	0.398	0.283	0.360	0.111	0.177	0.038
23	0.015	0.018	0.774	1.36	0.774	0.662	0.398	0.283	0.322	0.077	0.207	0.038
24	0.015	0.018	0.718	1.54	0.774	0.662	0.398	0.283	0.283	0.038	0.207	0.038
25	0.015	0.018	0.718	2.78	0.718	0.662	0.398	0.283	0.283	0.038	0.283	0.038
26	0.015	3.81	0.718	0.944	1.27	0.662	0.398	0.283	0.322	0.038	0.283	0.038
27	0.011	0.549	0.662	0.774	1.00	0.605	0.398	0.283	0.398	0.077	0.322	0.038
28	0.011	0.360	0.662	0.718	0.831	0.549	0.398	0.283	0.398	0.094	0.245	0.038
29	0.015	0.245	0.662	0.662	-----	0.549	0.398	0.283	0.398	0.094	0.207	0.038
30	0.018	0.207	0.662	0.662	-----	0.549	0.398	0.283	0.398	0.058	0.177	0.038
31	0.018	-----	0.662	0.605	-----	0.549	-----	0.283	-----	0.038	0.147	-----
Maks.	117.	13.3	33.7	5.60	13.0	41.9	0.887	0.436	2.45	1.45	0.322	0.360
Min.	0.001	0.015	0.147	0.605	0.492	0.003	0.398	0.245	0.147	0.038	0.025	0.038
Ortalama	0.212	0.225	0.698	0.825	1.05	1.50	0.439	0.339	0.288	0.156	0.170	0.080
LT/SN/Km2	1.72	1.83	5.67	6.70	8.56	12.2	3.57	2.75	2.34	1.27	1.38	0.647
AKIM mm.	4.62	4.75	15.2	18.0	20.7	32.6	9.25	7.38	6.08	3.39	3.69	1.68
MİL. M3	0.568	0.584	1.87	2.21	2.55	4.01	1.14	0.908	0.747	0.417	0.454	0.206

SU YILI (2006) YILLIK TOPLAM AKIM 15.66 MİLYON M3 127 MM. 4.0 LT/SN/Km2

07. Büyük Menderes Havzasi

D07A081 BÜYÜK MENDERES NEHRİ. SARAYKÖY KÖPRÜSÜ

YERİ : SARAYKÖY-AYDIN KARAYOLUNUN 4.KM.SİNDE BÜYÜK MENDERES NEHRİ,ÜZERİNDEKİ ESKİ KÖPRÜNÜN 10M.MENBASINDADIR.
28°55'2" Doğu - 37°57'9" Kuzey

YAĞIŞ ALANI : 11852,00 km2 **YAKLAŞIK KOT** : 130 m

GÖZLEM SÜRESİ : 12.08.1980 - 30.09.2006

ORTALAMA AKIMLAR : Gözlem süresinde 17.835 m3/sn. (16 Yıllık) 2006 Su yılında 17.835 m3/sn.

ANLIK EN ÇOK VE EN AZ AKIMLAR:

2006 Su yılında anlık ençok akım	:	71.2	m3/sn	04.07.2006
2006 Su yılında anlık enaz akım	:	2.60	m3/sn	25.04.2006
Gözlem süresinde anlık ençok akım	:	260.	m3/sn	12.02.1984
Gözlem süresinde anlık enaz akım	:	0.263	m3/sn	14.09.1992

Akımlar 01 Ekim 2005 'den 30 Eylül 2006' a kadar m3/sn olarak

Gün	Ekim	Kasım	Aralık	Ocak	Şubat	Mart	Nisan	Mayıs	Haziran	Temmuz	Ağustos	Eylül
01	9.80	10.5	13.6	12.2	13.2	11.2	11.8	5.90	13.2	43.5	40.8	35.0
02	19.2	10.5	12.2	12.5	13.6	10.8	11.2	10.5	9.80	38.4	41.1	38.0
03	17.8	11.2	11.8	12.9	13.6	10.5	9.52	7.76	8.96	45.1	30.1	35.4
04	12.5	12.2	11.5	12.9	13.2	10.5	8.40	8.96	9.24	61.3	38.4	33.9
05	11.2	11.2	11.8	13.2	13.2	10.1	8.08	12.9	10.1	47.5	40.0	29.4
06	10.8	10.8	11.8	16.0	14.6	9.80	7.44	8.08	12.2	40.8	39.6	24.5
07	10.5	10.8	11.8	13.6	16.4	9.80	5.90	6.50	12.5	44.7	39.6	24.5
08	10.5	11.5	11.8	12.9	15.7	12.5	5.60	5.60	11.8	44.7	39.6	24.5
09	10.1	10.8	11.5	12.5	15.7	13.6	5.02	5.60	27.9	43.9	39.2	24.5
10	9.80	9.80	11.8	12.2	15.3	10.8	5.02	5.90	26.4	43.5	38.0	24.5
11	10.1	9.52	11.8	11.8	17.4	10.5	5.60	6.50	27.5	42.7	34.6	30.5
12	9.80	10.8	11.8	12.2	18.1	10.5	5.02	6.20	26.8	41.1	24.2	30.1
13	9.52	11.2	11.5	11.8	17.1	13.9	4.18	6.20	26.8	40.8	33.9	30.5
14	9.52	10.8	11.8	11.8	15.7	18.5	4.18	5.60	23.4	42.7	33.5	29.0
15	9.24	10.8	12.5	11.8	15.3	16.4	7.44	5.02	15.3	41.5	32.3	22.4
16	9.24	10.8	12.5	12.2	14.6	14.6	4.74	4.18	19.9	40.0	32.3	24.2
17	10.5	10.8	11.8	12.2	14.3	13.9	4.18	6.20	19.2	40.4	31.6	23.8
18	10.5	14.6	12.2	12.2	14.3	13.9	4.18	9.24	17.1	39.6	33.1	19.2
19	10.8	12.5	25.3	12.5	14.3	13.9	3.90	12.5	17.8	38.0	31.2	15.0
20	10.8	15.0	18.8	16.0	14.3	13.6	5.02	11.5	22.0	36.9	30.8	10.8
21	10.8	12.9	14.6	13.2	14.3	13.6	4.46	11.5	31.2	39.6	30.5	9.80
22	10.5	12.2	14.3	12.9	14.3	13.6	4.46	11.5	25.3	38.4	29.7	9.80
23	9.80	12.2	13.9	12.9	13.9	13.6	4.18	10.5	24.5	38.4	24.5	10.1
24	9.52	12.2	13.2	13.6	11.8	12.9	4.74	11.5	35.8	40.0	24.2	10.8
25	8.96	12.2	12.9	16.7	10.1	17.8	3.64	11.5	34.2	41.1	30.8	20.9
26	9.24	16.0	12.9	17.4	11.2	13.9	3.38	6.80	39.6	40.8	30.5	12.5
27	8.96	14.6	12.5	27.9	11.2	12.5	4.46	7.12	53.7	40.4	30.8	9.80
28	13.2	14.6	12.9	22.7	11.2	12.2	4.74	8.08	47.5	40.0	30.8	8.68
29	18.5	15.0	12.9	16.0	-----	11.8	5.90	9.52	47.1	40.4	34.2	8.08
30	18.5	14.6	12.9	13.9	-----	12.2	5.30	11.8	46.7	40.4	34.2	8.96
31	16.7	-----	12.9	13.6	-----	12.5	-----	13.2	-----	40.4	35.4	-----
Maks.	30.1	20.2	33.9	43.1	18.8	22.0	12.2	20.2	64.5	71.2	42.7	40.0
Min.	8.68	9.52	11.2	11.5	10.1	9.52	2.60	3.90	8.08	18.5	13.2	6.80
Ortalama	11.5	12.1	13.1	14.1	14.2	12.8	5.72	8.51	24.8	41.8	33.5	21.3
LT/SN/Km2	0.971	1.02	1.10	1.19	1.20	1.08	0.483	0.718	2.09	3.53	2.83	1.80
AKIM mm.	2.60	2.64	2.96	3.18	2.90	2.89	1.25	1.92	5.42	9.46	7.58	4.66
MİL. M3	30.8	31.3	35.0	37.7	34.4	34.2	14.8	22.8	64.2	112.	89.8	55.2

SU YILI (2006) YILLIK TOPLAM AKIM 562.20 MİLYON M3 47 MM. 1.5 LT/SN/Km2

07. Büyük Menderes Havzasi

D07A082 MADRAN ÇAYI. KASAR

YERİ : **AYDIN-ÇINE KARAYOLU ÜSTÜNDE TOPCAM BARAJIN'DAN SOLA AYRILAN YOLUN 11.KM SINDEKI KASAR KOYUNE 3 KM.MESAFEDEDİR.**
28°2'29" Doğu - 37°44'24" Kuzey

YAĞIŞ ALANI : **184,00 km2** **YAKLAŞIK KOT : 111 m**

GÖZLEM SÜRESİ : **16.11.1982 - 30.09.2006**

ORTALAMA AKIMLAR : **Gözlem süresinde 1.203 m3/sn. (16 Yıllık) 2006 Su yılında 1.573 m3/sn.**

ANLIK EN ÇOK VE EN AZ AKIMLAR:

2006 Su yılında anlık ençok akım	:	**76.4**	**m3/sn**	**14.03.2006**
2006 Su yılında anlık enaz akım	:	**0.000**	**m3/sn**	**01.10.2005**
Gözlem süresinde anlık ençok akım	:	**86.0**	**m3/sn**	**20.01.1985**
Gözlem süresinde anlık enaz akım	:	**0.000**	**m3/sn**	**01.10.1983**

Akımlar 01 Ekim 2005 'den 30 Eylül 2006' a kadar m3/sn olarak

Gün	Ekim	Kasım	Aralık	Ocak	Şubat	Mart	Nisan	Mayıs	Haziran	Temmuz	Ağustos	Eylül
01	KURU	0.026	0.268	1.10	1.20	2.59	1.91	0.500	0.048	0.026	KURU	KURU
02	KURU	0.026	0.235	0.800	1.57	2.25	1.57	0.400	0.048	0.026	KURU	KURU
03	0.070	0.026	0.202	0.600	1.20	2.08	1.57	0.400	0.048	0.037	KURU	KURU
04	0.136	0.026	0.202	0.500	0.900	1.91	1.57	0.400	0.037	0.334	KURU	KURU
05	0.070	0.026	0.202	0.500	0.900	1.57	2.08	0.367	0.037	0.169	KURU	KURU
06	0.059	0.037	0.169	1.91	8.35	1.40	1.74	0.367	0.037	0.103	KURU	KURU
07	0.048	0.048	0.169	1.74	37.5	2.08	1.40	0.500	0.026	0.059	KURU	KURU
08	0.048	0.048	0.169	1.40	23.8	17.8	1.20	0.400	0.026	0.037	KURU	KURU
09	0.037	0.059	0.169	1.20	6.44	14.0	1.20	0.367	0.026	0.026	KURU	KURU
10	0.037	0.059	0.169	0.900	9.40	6.96	1.20	0.334	0.026	0.015	KURU	KURU
11	0.026	0.059	0.169	0.700	28.1	4.94	1.10	0.334	0.037	0.015	KURU	KURU
12	0.026	0.059	0.169	0.600	26.4	6.18	1.00	0.301	0.037	0.010	KURU	KURU
13	0.026	0.059	0.169	0.500	12.2	19.8	0.800	0.301	0.037	0.010	KURU	KURU
14	0.026	0.059	0.169	0.400	6.96	41.4	1.00	0.301	0.037	KURU	KURU	KURU
15	0.026	0.059	0.169	0.367	4.94	17.8	1.57	0.268	0.037	KURU	KURU	KURU
16	0.026	0.059	0.235	0.334	3.79	10.5	1.20	0.268	0.037	KURU	KURU	KURU
17	0.026	0.059	0.202	0.334	3.56	7.22	0.900	0.235	0.037	KURU	KURU	KURU
18	0.026	0.400	0.700	0.301	4.48	6.44	0.800	0.235	0.037	KURU	KURU	KURU
19	0.026	0.400	13.6	2.25	3.79	6.44	0.700	0.202	0.037	KURU	KURU	KURU
20	0.026	1.10	2.59	7.22	3.56	5.40	0.700	0.202	0.037	KURU	KURU	KURU
21	0.026	0.500	1.00	2.93	3.10	4.71	0.600	0.169	0.037	KURU	KURU	KURU
22	0.026	0.301	0.600	1.91	2.59	4.48	0.600	0.169	0.026	KURU	KURU	KURU
23	0.026	0.202	0.500	2.76	2.42	4.25	0.900	0.169	0.026	KURU	KURU	KURU
24	0.015	0.202	0.400	4.02	2.25	4.25	0.900	0.136	0.026	KURU	KURU	KURU
25	0.015	0.367	0.334	15.0	2.76	3.56	0.700	0.136	0.026	KURU	KURU	KURU
26	0.015	7.74	0.301	6.44	2.42	3.10	0.600	0.136	0.037	KURU	KURU	KURU
27	0.015	2.25	0.268	3.10	2.25	2.76	0.500	0.103	0.334	KURU	KURU	KURU
28	0.015	0.600	0.268	2.25	2.08	2.42	0.500	0.103	0.136	KURU	KURU	KURU
29	0.015	0.367	0.334	1.74	-----	2.25	0.500	0.070	0.070	KURU	KURU	KURU
30	0.015	0.301	1.30	1.30	-----	2.08	0.500	0.059	0.037	KURU	KURU	KURU
31	0.015	-----	0.700	1.20	-----	1.91	-----	0.048	-----	KURU	KURU	-----
Maks.	0.202	12.2	23.8	22.2	37.5	76.4	2.42	0.600	0.600	0.700	KURU	KURU
Min.	KURU	0.026	0.169	0.301	0.900	1.30	0.500	0.048	0.026	KURU	KURU	KURU
Ortalama	0.031	0.517	0.843	2.14	7.46	6.92	1.05	0.257	0.049	0.028	KURU	KURU
LT/SN/Km2	0.169	2.81	4.58	11.6	40.5	37.6	5.71	1.40	0.269	0.152	0.000	0.000
AKIM mm.	0.452	7.29	12.3	31.1	98.1	101.	14.8	3.75	0.697	0.407	0.000	0.000
MİL. M3	0.083	1.34	2.26	5.73	18.0	18.5	2.72	0.689	0.128	0.075	0.000	0.000

SU YILI (2006) YILLIK TOPLAM AKIM 49.52 MİLYON M3 269 MM. 8.5 LT/SN/Km2

07. Büyük Menderes Havzasi

D07A083 YENİDERE ÇALIKÖY KÖPRÜSÜ

YERİ : **KARACASU-TAVAS YOLUNUN KARACAHİSARDAN SAĞA AYRILAN YOLUN3.KM SİNDEKİ ÇALIKÖY KÖPRÜSÜNDEDİR**

28°55'23" Doğu - 37°35'36" Kuzey

YAĞIŞ ALANI : **668,30 km2** **YAKLAŞIK KOT : 855 m**

GÖZLEM SÜRESİ : **23.12.1982 - 30.09.2006**

ORTALAMA AKIMLAR : **Gözlem süresinde 1.250 m3/sn. (27 Yıllık) 2006 Su yılında 0.656 m3/sn.**

ANLIK EN ÇOK VE EN AZ AKIMLAR:

2006 Su yılında anlık ençok akım	:	**28.2**	**m3/sn**	**14.03.2006**
2006 Su yılında anlık enaz akım	:	**0.173**	**m3/sn**	**03.10.2005**
Gözlem süresinde anlık ençok akım	:	**87.0**	**m3/sn**	**25.01.1984**
Gözlem süresinde anlık enaz akım	:	**0.000**	**m3/sn**	**15.05.1987**

Akımlar 01 Ekim 2005 'den 30 Eylül 2006' a kadar m3/sn olarak

Gün	Ekim	Kasım	Aralık	Ocak	Şubat	Mart	Nisan	Mayıs	Haziran	Temmuz	Ağustos	Eylül
01	0.273	0.273	0.317	0.252	0.403	0.571	1.59	1.08	0.537	0.403	0.295	0.252
02	0.317	0.295	0.317	0.252	0.437	0.537	1.59	1.03	0.537	0.470	0.295	0.252
03	0.252	0.295	0.317	0.252	0.403	0.470	1.59	1.03	0.537	0.437	0.295	0.252
04	0.209	0.317	0.317	0.252	0.403	0.437	1.77	1.08	0.537	0.437	0.295	0.252
05	0.209	0.317	0.317	0.295	0.403	0.437	2.67	1.65	0.571	0.705	0.273	0.252
06	0.209	0.317	0.317	0.470	1.65	0.437	1.53	1.22	0.605	0.638	0.273	0.252
07	0.209	0.338	0.317	0.437	3.43	0.437	1.40	1.12	0.470	0.571	0.273	0.252
08	0.209	0.360	0.317	0.338	4.19	1.08	1.40	1.08	0.470	0.504	0.273	0.252
09	0.209	0.360	0.317	0.338	2.51	2.21	1.34	1.08	0.470	0.437	0.273	0.252
10	0.230	0.360	0.317	0.338	1.03	1.17	1.34	0.883	0.470	0.360	0.273	0.252
11	0.252	0.360	0.317	0.338	1.59	1.03	1.34	0.705	0.360	0.360	0.273	0.295
12	0.273	0.360	0.317	0.317	4.41	1.03	1.28	0.672	0.360	0.360	0.273	0.295
13	0.273	0.360	0.317	0.317	1.59	2.43	1.28	0.705	0.360	0.360	0.273	0.295
14	0.252	0.360	0.317	0.317	0.980	14.0	1.40	0.672	0.338	0.360	0.273	0.295
15	0.252	0.360	0.338	0.317	0.835	4.30	1.77	0.672	0.295	0.360	0.273	0.295
16	0.252	0.360	0.338	0.317	0.739	2.58	1.34	0.672	0.252	0.338	0.273	0.295
17	0.252	0.360	0.338	0.317	0.739	2.36	1.28	0.672	0.252	0.317	0.252	0.295
18	0.252	0.360	0.360	0.317	0.739	2.13	1.22	0.672	0.252	0.360	0.252	0.295
19	0.252	0.360	0.835	0.317	0.739	2.21	1.17	0.638	0.295	0.317	0.252	0.295
20	0.252	0.360	0.437	0.381	0.787	1.91	1.22	0.638	0.295	0.317	0.252	0.295
21	0.252	0.360	0.317	0.381	0.787	1.77	1.17	0.638	0.295	0.317	0.252	0.295
22	0.252	0.360	0.295	0.338	0.739	1.71	1.17	0.672	0.295	0.317	0.252	0.295
23	0.252	0.317	0.295	0.317	0.705	1.71	1.34	0.638	0.295	0.295	0.252	0.295
24	0.273	0.295	0.295	0.338	0.672	1.71	1.46	0.672	0.295	0.295	0.252	0.295
25	0.273	0.295	0.252	0.931	0.672	1.71	1.08	0.605	0.295	0.295	0.252	0.403
26	0.273	0.338	0.252	0.638	0.672	1.71	1.03	0.605	0.273	0.295	0.252	0.403
27	0.273	0.317	0.252	0.470	0.672	1.65	1.03	0.571	0.273	0.295	0.252	0.403
28	0.273	0.317	0.252	0.403	0.672	1.65	1.03	0.571	0.437	0.295	0.252	0.403
29	0.273	0.317	0.252	0.403	-----	1.59	1.08	0.537	0.437	0.295	0.252	0.403
30	0.273	0.317	0.252	0.403	-----	1.59	1.08	0.537	0.437	0.295	0.252	0.537
31	0.273	-----	0.252	0.403	-----	1.59	-----	0.537	-----	0.295	0.252	-----
Maks.	0.931	0.403	1.65	1.28	6.32	28.2	4.87	2.92	0.672	0.705	0.295	0.537
Min.	0.173	0.273	0.252	0.230	0.403	0.437	1.03	0.504	0.209	0.295	0.230	0.230
Ortalama	0.253	0.336	0.324	0.371	1.20	1.94	1.37	0.792	0.386	0.377	0.266	0.307
LT/SN/Km2	0.378	0.502	0.485	0.555	1.80	2.90	2.04	1.19	0.578	0.565	0.398	0.459
AKIM mm.	1.01	1.30	1.30	1.49	4.34	7.78	5.30	3.17	1.50	1.51	1.06	1.19
MİL. M3	0.676	0.870	0.868	0.994	2.90	5.20	3.54	2.12	1.00	1.01	0.712	0.795

SU YILI (2006) YILLIK TOPLAM AKIM 20.68 MİLYON M3 31 MM. 1.0 LT/SN/Km2

07. Büyük Menderes Havzasi

D07A087 KESTEL D. KIZILCA

YERİ : **SANDIKLI-HOCALAR ASFALTI TAKİP EDİLEREK BAŞTEPE KÖYÜNDEN SORKUN KASABASI YÖNÜNE GIDILIR. ORMAN DEPOSUNDAN SOLA DÖNÜLÜR 7 KM SONRA AGI YE VARILIR.HARİTA PAFTA NO: L24-A1 30°4'34" Doğu - 38°23'33" Kuzey**

YAĞIŞ ALANI : **46,20 km2** **YAKLAŞIK KOT : 1067 m**

GÖZLEM SÜRESİ : **01.10.1985 - 30.09.2006**

ORTALAMA AKIMLAR : **Gözlem süresinde 0.392 m3/sn. (21 Yıllık) 2006 Su yılında 0.285 m3/sn.**

ANLIK EN ÇOK VE EN AZ AKIMLAR:

2006 Su yılında anlık ençok akım	:	**4.80**	**m3/sn**	**11.02.2006**
2006 Su yılında anlık enaz akım	:	**0.000**	**m3/sn**	**01.10.2005**
Gözlem süresinde anlık ençok akım	:	**26.0**	**m3/sn**	**17.12.2001**
Gözlem süresinde anlık enaz akım	:	**0.000**	**m3/sn**	**07.08.1990**

3. Anahtar Eğrisi (Seviyeler cm olarak)

Seviye	Akım	Seviye	Akım	Seviye	Akım	Seviye	Akım
1	0.000	16	0.490	31	2.5	36	3.4
4	0.004	19	0.760	32	2.6	37	3.6
7	0.028	22	1.1	33	2.8	41	4.5
10	0.105	25	1.5	34	3.0	51	6.4
13	0.270	28	2.0	35	3.2	111	29.0

Akımlar 01 Ekim 2005 'den 30 Eylül 2006' a kadar m3/sn olarak

Gün	Ekim	Kasım	Aralık	Ocak	Şubat	Mart	Nisan	Mayıs	Haziran	Temmuz	Ağustos	Eylül
01	KURU	KURU	0.014	0.175	0.090	1.80	0.490	0.200	0.074	0.007	KURU	KURU
02	KURU	KURU	0.014	0.090	0.130	1.65	0.400	0.150	0.050	0.007	KURU	KURU
03	KURU	KURU	0.014	0.064	0.175	2.80	0.400	0.150	0.050	0.007	KURU	KURU
04	KURU	KURU	0.014	0.043	0.230	2.40	0.325	0.105	0.050	0.007	KURU	KURU
05	KURU	KURU	0.014	0.130	0.175	1.52	0.325	0.105	0.028	0.007	KURU	KURU
06	KURU	KURU	0.014	0.230	0.720	1.12	0.270	0.105	0.028	0.007	KURU	KURU
07	KURU	KURU	0.014	0.130	1.50	0.990	0.270	0.105	0.015	KURU	KURU	KURU
08	KURU	KURU	0.014	0.090	1.40	1.12	0.270	0.105	0.015	KURU	KURU	KURU
09	KURU	KURU	0.005	0.064	0.820	1.25	0.325	0.105	0.015	KURU	KURU	KURU
10	KURU	KURU	0.001	0.043	1.40	1.12	0.270	0.105	0.015	KURU	KURU	KURU
11	KURU	KURU	0.001	0.026	4.80	1.25	0.200	0.105	0.015	KURU	KURU	KURU
12	KURU	KURU	0.001	0.026	4.10	1.52	0.200	0.105	0.015	KURU	KURU	KURU
13	KURU	KURU	0.001	0.026	1.80	3.20	0.200	0.105	0.015	KURU	KURU	KURU
14	KURU	KURU	0.001	0.014	1.05	4.50	0.490	0.105	0.015	KURU	KURU	KURU
15	KURU	KURU	0.001	0.014	0.620	3.55	1.38	0.105	0.015	KURU	KURU	KURU
16	KURU	KURU	0.001	0.014	0.450	2.40	0.670	0.400	0.015	KURU	KURU	KURU
17	KURU	KURU	0.001	0.014	0.300	1.65	0.490	0.400	0.015	KURU	KURU	KURU
18	KURU	KURU	0.043	0.014	0.530	1.25	0.400	0.270	0.015	KURU	KURU	KURU
19	KURU	0.015	1.15	0.043	0.930	1.25	0.270	0.270	0.015	KURU	KURU	KURU
20	KURU	0.450	0.530	0.620	1.15	1.12	0.270	0.200	0.015	KURU	KURU	KURU
21	KURU	0.130	0.130	0.175	1.40	1.12	0.200	0.150	0.015	KURU	KURU	KURU
22	KURU	0.043	0.064	0.130	1.40	1.12	0.200	0.105	0.015	KURU	KURU	KURU
23	KURU	0.026	0.043	0.230	1.25	1.12	0.325	0.105	0.015	KURU	KURU	KURU
24	KURU	0.014	0.043	0.175	1.50	1.12	0.670	0.105	0.007	KURU	KURU	KURU
25	KURU	0.014	0.026	0.130	1.80	0.990	0.400	0.105	0.007	KURU	KURU	KURU
26	KURU	0.230	0.026	0.130	1.65	0.890	0.270	0.105	0.007	KURU	KURU	KURU
27	KURU	0.130	0.026	0.090	1.40	0.760	0.200	0.105	0.007	KURU	KURU	KURU
28	KURU	0.043	0.026	0.090	1.38	0.670	0.200	0.074	0.007	KURU	KURU	KURU
29	KURU	0.026	0.090	0.090	-----	0.580	0.200	0.074	0.007	KURU	KURU	KURU
30	KURU	0.026	0.130	0.090	-----	0.580	0.150	0.074	0.007	KURU	KURU	KURU
31	KURU	-----	0.130	0.090	-----	0.580	-----	0.074	-----	KURU	KURU	-----
Maks.	KURU	0.450	3.00	0.620	4.80	4.50	1.38	0.400	0.074	0.007	KURU	KURU
Min.	KURU	KURU	0.001	0.014	0.090	0.580	0.150	0.074	0.007	KURU	KURU	KURU
Ortalama	KURU	0.038	0.083	0.106	1.22	1.52	0.358	0.141	0.019	0.001	KURU	KURU
LT/SN/Km2	0.000	0.828	1.80	2.30	26.4	32.8	7.74	3.06	0.421	0.029	0.000	0.000
AKIM mm.	0.000	2.15	4.83	6.15	63.9	87.9	20.1	8.18	1.09	0.079	0.000	0.000
MİL. M3	0.000	0.099	0.223	0.284	2.95	4.06	0.927	0.378	0.050	0.004	0.000	0.000

SU YILI (2006) YILLIK TOPLAM AKIM 8.98 MİLYON M3 194 MM. 6.2 LT/SN/Km2

07. Büyük Menderes Havzasi

D07A093 KORKOZ DERESİ. DEĞİRMENBÜKÜ

YERİ : **KARACASU-TAVAS YOLUNUN 20.KM SİNDE DEĞİRMENBÜKÜ MEVKİİNDEDİR.**
28°48'43" Doğu - 37°41'9" Kuzey

YAĞIŞ ALANI : **72,10 km2** **YAKLAŞIK KOT : 690 m**

GÖZLEM SÜRESİ : **04.10.1986 - 30.09.2006**

ORTALAMA AKIMLAR : **Gözlem süresinde 0.061 m3/sn. (12 Yıllık) 2006 Su yılında 0.044 m3/sn.**

ANLIK EN ÇOK VE EN AZ AKIMLAR:

2006 Su yılında anlık ençok akım	**:**	**1.49 m3/sn**	**13.03.2006**
2006 Su yılında anlık enaz akım	**:**	**0.002 m3/sn**	**12.06.2006**
Gözlem süresinde anlık ençok akım	**:**	**9.88 m3/sn**	**30.05.2005**
Gözlem süresinde anlık enaz akım	**:**	**0.000 m3/sn**	**01.10.1990**

Akımlar 01 Ekim 2005 'den 30 Eylül 2006' a kadar m3/sn olarak

Gün	Ekim	Kasım	Aralık	Ocak	Şubat	Mart	Nisan	Mayıs	Haziran	Temmuz	Ağustos	Eylül
01	0.030	0.005	0.012	0.066	0.066	0.066	0.102	0.066	0.030	0.012	0.005	0.005
02	0.030	0.005	0.012	0.066	0.066	0.066	0.102	0.030	0.030	0.012	0.005	0.005
03	0.030	0.005	0.012	0.066	0.066	0.066	0.030	0.030	0.030	0.012	0.005	0.005
04	0.030	0.005	0.012	0.066	0.066	0.048	0.030	0.030	0.030	0.012	0.005	0.005
05	0.030	0.005	0.012	0.066	0.066	0.048	0.030	0.030	0.030	0.048	0.005	0.005
06	0.030	0.005	0.012	0.066	0.196	0.066	0.030	0.030	0.030	0.048	0.005	0.005
07	0.030	0.005	0.012	0.066	0.720	0.720	0.030	0.030	0.030	0.048	0.005	0.005
08	0.030	0.005	0.012	0.066	0.310	0.272	0.030	0.030	0.030	0.048	0.005	0.005
09	0.030	0.005	0.012	0.066	0.120	0.102	0.030	0.030	0.030	0.048	0.005	0.005
10	0.030	0.005	0.012	0.066	0.102	0.102	0.030	0.030	0.030	0.048	0.005	0.005
11	0.030	0.005	0.012	0.066	0.102	0.102	0.030	0.030	0.030	0.005	0.005	0.005
12	0.030	0.005	0.012	0.066	0.102	0.120	0.030	0.030	0.002	0.005	0.005	0.005
13	0.030	0.005	0.012	0.066	0.102	0.474	0.030	0.030	0.002	0.005	0.005	0.005
14	0.030	0.005	0.012	0.066	0.102	0.932	0.066	0.030	0.012	0.005	0.005	0.005
15	0.030	0.005	0.012	0.066	0.102	0.196	0.066	0.030	0.012	0.005	0.005	0.005
16	0.030	0.005	0.012	0.066	0.102	0.158	0.066	0.030	0.012	0.005	0.005	0.005
17	0.030	0.005	0.012	0.066	0.102	0.158	0.066	0.030	0.012	0.005	0.005	0.005
18	0.030	0.005	0.012	0.066	0.102	0.158	0.066	0.030	0.012	0.005	0.005	0.005
19	0.030	0.030	0.012	0.066	0.102	0.102	0.066	0.030	0.012	0.005	0.005	0.005
20	0.030	0.030	0.012	0.066	0.084	0.102	0.066	0.030	0.002	0.005	0.005	0.005
21	0.030	0.030	0.012	0.066	0.084	0.102	0.066	0.030	0.002	0.005	0.005	0.005
22	0.030	0.030	0.012	0.066	0.084	0.102	0.066	0.030	0.002	0.005	0.005	0.005
23	0.012	0.030	0.012	0.066	0.084	0.102	0.066	0.030	0.002	0.005	0.005	0.005
24	0.005	0.030	0.012	0.066	0.084	0.102	0.066	0.030	0.005	0.005	0.005	0.005
25	0.005	0.030	0.012	0.066	0.084	0.102	0.066	0.030	0.005	0.005	0.005	0.005
26	0.012	0.030	0.012	0.066	0.084	0.102	0.066	0.030	0.005	0.005	0.005	0.005
27	0.005	0.030	0.012	0.066	0.066	0.102	0.066	0.030	0.012	0.005	0.005	0.005
28	0.005	0.030	0.012	0.066	0.066	0.102	0.066	0.030	0.012	0.005	0.005	0.005
29	0.005	0.030	0.012	0.066	-----	0.102	0.066	0.030	0.012	0.005	0.005	0.005
30	0.005	0.030	0.012	0.066	-----	0.102	0.066	0.030	0.012	0.005	0.005	0.005
31	0.005	-----	0.012	0.066	-----	0.102	-----	0.030	-----	0.005	0.005	-----
Maks.	0.030	0.030	0.012	0.066	1.14	1.49	0.102	0.066	0.030	0.048	0.005	0.005
Min.	0.005	0.005	0.012	0.066	0.066	0.048	0.030	0.030	0.002	0.005	0.005	0.005
Ortalama	0.023	0.015	0.012	0.066	0.122	0.167	0.055	0.031	0.016	0.014	0.005	0.005
LT/SN/Km2	0.322	0.208	0.166	0.915	1.69	2.32	0.766	0.432	0.221	0.197	0.069	0.069
AKIM mm.	0.862	0.539	0.446	2.45	4.09	6.21	1.98	1.16	0.572	0.528	0.186	0.180
MİL. M3	0.062	0.039	0.032	0.177	0.295	0.448	0.143	0.083	0.041	0.038	0.013	0.013

SU YILI (2006) YILLIK TOPLAM AKIM 1.38 MİLYON M3 19 MM. 0.6 LT/SN/Km2

07. Büyük Menderes Havzasi

D07A096 GEVENEZ DERSİ. GEVENEZ

YERİ : **MUĞLA-AYDIN KARAYOLUNUN 15.KM SİNDEN SOLA AYRILAN KARAKUYU YOLUNDAN 20.KM.GEVENEZ KÖYÜNDEKİ KÖPRÜDEDİR.**
28°8'15" Doğu - 37°14'36" Kuzey

YAĞIŞ ALANI : **41,00 km2** **YAKLAŞIK KOT : 450 m**

GÖZLEM SÜRESİ : **02.12.1987 - 30.09.2006**

ORTALAMA AKIMLAR : **Gözlem süresinde 0.323 m3/sn. (16 Yıllık) 2006 Su yılında 0.309 m3/sn.**

ANLIK EN ÇOK VE EN AZ AKIMLAR:

2006 Su yılında anlık ençok akım	**:**	**35.6**	**m3/sn**	**18.12.2005**
2006 Su yılında anlık enaz akım	**:**	**0.000**	**m3/sn**	**01.10.2005**
Gözlem süresinde anlık ençok akım	**:**	**91.8**	**m3/sn**	**17.12.2001**
Gözlem süresinde anlık enaz akım	**:**	**0.000**	**m3/sn**	**01.11.1987**

Akımlar 01 Ekim 2005 'den 30 Eylül 2006' a kadar m3/sn olarak

Gün	Ekim	Kasım	Aralık	Ocak	Şubat	Mart	Nisan	Mayıs	Haziran	Temmuz	Ağustos	Eylül
01	KURU	0.034	0.177	0.155	0.288	0.659	0.456	0.089	0.034	0.034	0.025	KURU
02	0.011	0.034	0.177	0.155	0.288	0.420	0.420	0.111	0.034	0.034	0.025	KURU
03	KURU	0.034	0.177	0.155	0.288	0.420	0.383	0.111	0.034	0.034	0.025	KURU
04	KURU	0.034	0.177	0.155	0.288	0.383	0.347	0.089	0.034	0.034	0.011	KURU
05	KURU	0.034	0.177	0.347	0.288	0.383	0.310	0.089	0.034	0.047	KURU	KURU
06	KURU	0.034	0.133	0.420	0.603	0.383	0.288	0.089	0.034	0.034	KURU	KURU
07	0.011	0.034	0.061	0.310	1.21	0.659	0.266	0.089	0.034	0.034	KURU	KURU
08	0.034	0.034	0.061	0.243	1.35	3.97	0.243	0.089	0.034	0.034	KURU	KURU
09	0.034	0.034	0.061	0.243	0.915	3.43	0.221	0.089	0.034	0.034	KURU	KURU
10	0.034	0.034	0.061	0.243	0.659	2.25	0.177	0.089	0.034	0.034	KURU	KURU
11	0.034	0.034	0.061	0.243	2.04	1.82	0.155	0.089	0.034	0.034	KURU	KURU
12	0.034	0.034	0.061	0.155	1.50	2.25	0.133	0.089	0.047	0.034	KURU	KURU
13	0.034	0.034	0.061	0.155	1.13	8.44	0.155	0.089	0.047	0.034	KURU	KURU
14	0.034	0.034	0.061	0.155	0.769	7.39	0.199	0.089	0.047	0.034	KURU	KURU
15	0.034	0.034	0.155	0.155	0.548	3.19	0.199	0.089	0.034	0.034	KURU	KURU
16	0.034	0.034	0.075	0.155	0.456	2.14	0.155	0.089	0.034	0.034	KURU	KURU
17	0.034	0.047	0.061	0.155	0.420	1.93	0.155	0.089	0.034	0.034	KURU	KURU
18	0.034	0.288	1.06	0.155	0.420	1.82	0.155	0.089	0.034	0.034	KURU	KURU
19	0.034	0.155	5.33	0.155	0.420	1.71	0.133	0.089	0.034	0.034	KURU	KURU
20	0.034	0.221	1.50	0.266	0.420	1.50	0.133	0.089	0.034	0.034	KURU	KURU
21	0.034	0.111	0.769	0.243	0.420	1.35	0.133	0.089	0.075	0.034	KURU	KURU
22	0.034	0.089	0.493	0.243	0.383	1.21	0.133	0.089	0.061	0.034	KURU	KURU
23	0.034	0.089	0.266	1.28	0.383	1.06	0.133	0.089	0.034	0.034	KURU	KURU
24	0.034	0.089	0.199	1.28	0.383	0.988	0.133	0.047	0.025	0.034	KURU	KURU
25	0.034	0.089	0.177	1.93	0.347	0.915	0.111	0.034	0.025	0.034	KURU	KURU
26	0.034	2.14	0.177	0.988	0.347	0.842	0.111	0.034	0.034	0.034	KURU	KURU
27	0.034	0.310	0.155	0.548	0.347	0.769	0.089	0.034	0.047	0.025	KURU	KURU
28	0.034	0.221	0.155	0.456	0.347	0.714	0.089	0.034	0.034	0.025	KURU	KURU
29	0.034	0.199	0.155	0.347	-----	0.659	0.111	0.034	0.034	0.025	KURU	KURU
30	0.034	0.177	0.155	0.288	-----	0.603	0.111	0.034	0.034	0.025	KURU	KURU
31	0.034	-----	0.155	0.288	-----	0.493	-----	0.034	-----	0.025	KURU	-----
Maks.	0.221	9.28	35.6	3.43	4.31	33.2	0.456	0.133	0.075	0.089	0.047	KURU
Min.	KURU	0.011	0.025	0.133	0.243	0.347	KURU	0.034	0.025	0.025	KURU	KURU
Ortalama	0.027	0.159	0.405	0.389	0.616	1.77	0.195	0.077	0.037	0.033	0.003	KURU
LT/SN/Km2	0.659	3.88	9.87	9.49	15.0	43.1	4.75	1.87	0.912	0.804	0.068	0.000
AKIM mm.	1.77	10.0	26.4	25.4	36.4	115.	12.3	5.01	2.36	2.15	0.181	0.000
MİL. M3	0.072	0.412	1.08	1.04	1.49	4.73	0.504	0.205	0.097	0.088	0.007	0.000

SU YILI (2006) YILLIK TOPLAM AKIM 9.72 MİLYON M3 237 MM. 7.5 LT/SN/Km2

07. Büyük Menderes Havzasi

D07A097 ELEKÇİ DERESİ. MADANLAR

YERİ : **MUĞLA-AYDIN YOLUNUN 25.KM SİNDEKİ YATAĞAN KAVŞAĞINDAN SAĞA AYRILAN ELEKÇİ YOLUNDAN 2.5 KM. MESAFEDEDİR.**
28°11'23" Doğu - 37°20'35" Kuzey

YAĞIŞ ALANI : **70,00 km2** **YAKLAŞIK KOT : 425 m**

GÖZLEM SÜRESİ : **26.10.1987 - 30.09.2006**

ORTALAMA AKIMLAR : **Gözlem süresinde 0.132 m3/sn. (15 Yıllık) 2006 Su yılında 0.123 m3/sn.**

ANLIK EN ÇOK VE EN AZ AKIMLAR:

2006 Su yılında anlık ençok akım	:	**6.14**	**m3/sn**	**02.10.2005**
2006 Su yılında anlık enaz akım	:	**0.000**	**m3/sn**	**04.08.2006**
Gözlem süresinde anlık ençok akım	:	**44.5**	**m3/sn**	**19.12.2002**
Gözlem süresinde anlık enaz akım	:	**0.000**	**m3/sn**	**01.10.1989**

Akımlar 01 Ekim 2005 'den 30 Eylül 2006' a kadar m3/sn olarak

Gün	Ekim	Kasım	Aralık	Ocak	Şubat	Mart	Nisan	Mayıs	Haziran	Temmuz	Ağustos	Eylül
01	0.001	0.008	0.029	0.048	0.085	0.261	0.203	0.099	0.035	0.022	0.004	0.001
02	0.793	0.008	0.022	0.048	0.085	0.203	0.203	0.085	0.029	0.022	0.004	0.001
03	0.188	0.008	0.022	0.048	0.070	0.203	0.203	0.085	0.029	0.114	0.004	0.001
04	0.048	0.012	0.022	0.035	0.070	0.203	0.261	0.085	0.029	0.129	0.001	0.001
05	0.029	0.008	0.022	0.042	0.070	0.203	0.261	0.085	0.029	0.035	0.001	0.001
06	0.019	0.008	0.022	0.114	0.159	0.203	0.203	0.085	0.029	0.019	0.001	0.001
07	0.012	0.008	0.015	0.099	0.665	0.377	0.173	0.085	0.029	0.012	0.001	0.001
08	0.008	0.008	0.012	0.085	1.14	0.708	0.144	0.085	0.022	0.012	0.001	0.001
09	0.008	0.008	0.012	0.085	0.406	0.665	0.114	0.085	0.022	0.012	0.001	0.001
10	0.008	0.008	0.012	0.055	0.579	0.579	0.099	0.085	0.022	0.012	0.001	0.001
11	0.012	0.008	0.012	0.055	1.63	0.493	0.085	0.085	0.022	0.012	0.001	KURU
12	0.015	0.008	0.012	0.048	1.25	0.493	0.099	0.085	0.022	0.012	0.001	KURU
13	0.012	0.008	0.012	0.048	0.708	1.36	0.085	0.085	0.022	0.005	0.001	KURU
14	0.008	0.008	0.012	0.048	0.493	1.88	0.159	0.085	0.022	0.005	0.001	KURU
15	0.008	0.008	0.019	0.035	0.348	1.47	0.173	0.085	0.022	0.005	0.001	KURU
16	0.008	0.008	0.022	0.035	0.203	1.20	0.203	0.085	0.022	0.005	0.001	KURU
17	0.008	0.008	0.019	0.035	0.203	0.836	0.188	0.070	0.022	0.005	0.001	KURU
18	0.008	0.085	0.019	0.035	0.319	0.750	0.173	0.070	0.022	0.005	0.001	KURU
19	0.008	0.022	1.96	0.035	0.261	0.665	0.159	0.070	0.022	0.005	0.001	KURU
20	0.008	0.042	0.203	0.035	0.290	0.579	0.144	0.070	0.022	0.005	0.001	KURU
21	0.008	0.015	0.144	0.035	0.203	0.493	0.144	0.055	0.029	0.005	0.001	KURU
22	0.008	0.012	0.144	0.035	0.203	0.435	0.144	0.055	0.029	0.005	0.001	KURU
23	0.008	0.008	0.085	0.070	0.188	0.377	0.144	0.048	0.029	0.005	0.001	KURU
24	0.008	0.008	0.042	0.261	0.188	0.348	0.129	0.048	0.022	0.005	0.001	0.001
25	0.008	0.008	0.042	1.20	0.188	0.348	0.114	0.048	0.022	0.005	0.001	0.002
26	0.008	0.793	0.029	0.319	0.203	0.348	0.099	0.042	0.022	0.005	0.001	0.001
27	0.008	0.070	0.029	0.173	0.203	0.319	0.099	0.035	0.022	0.005	0.001	0.001
28	0.008	0.042	0.029	0.129	0.203	0.290	0.085	0.035	0.022	0.005	0.001	0.001
29	0.008	0.029	0.070	0.114	-----	0.261	0.085	0.035	0.022	0.004	0.001	0.001
30	0.008	0.029	0.085	0.085	-----	0.203	0.085	0.035	0.022	0.004	0.001	0.001
31	0.008	-----	0.055	0.085	-----	0.203	-----	0.035	-----	0.004	0.001	-----
Maks.	6.14	4.26	6.00	2.95	2.38	1.88	0.261	0.099	0.042	4.17	0.015	0.005
Min.	0.001	0.008	0.012	0.029	0.070	0.203	0.085	0.029	0.022	0.005	KURU	KURU
Ortalama	0.042	0.043	0.104	0.115	0.379	0.547	0.149	0.069	0.025	0.016	0.001	0.001
LT/SN/Km2	0.598	0.620	1.49	1.65	5.41	7.81	2.12	0.979	0.350	0.233	0.018	0.009
AKIM mm.	1.60	1.61	3.99	4.41	13.1	20.9	5.50	2.62	0.908	0.623	0.049	0.022
MİL. M3	0.112	0.113	0.279	0.309	0.917	1.46	0.385	0.184	0.064	0.044	0.003	0.002

SU YILI (2006) YILLIK TOPLAM AKIM 3.87 MİLYON M3 55 MM. 1.8 LT/SN/Km2

07. Büyük Menderes Havzasi

D07A098 SIRAİNLER DERESI BAYIR

YERİ : **MUĞLA-AYDIN KARAYOLUNUN 15.KM SİNDEKİ BAYIR YERLEŞİM MERKEZİN'DEN KATRANCI EVLERİ MEVKİİNE GİDEN YOLDAN, YAKLAŞIK 5.KM MESAFEDEDİR. 28°15'0" Doğu - 37°17'1" Kuzey**

YAĞIŞ ALANI : **30,00 km2** **YAKLAŞIK KOT : 500 m**

GÖZLEM SÜRESİ : **07.07.1987 - 30.09.2006**

ORTALAMA AKIMLAR : **Gözlem süresinde 0.180 m3/sn. (19 Yıllık) 2006 Su yılında 0.157 m3/sn.**

ANLIK EN ÇOK VE EN AZ AKIMLAR:

2006 Su yılında anlık ençok akım	:	**8.92**	**m3/sn**	**14.03.2006**
2006 Su yılında anlık enaz akım	:	**0.000**	**m3/sn**	**01.10.2005**
Gözlem süresinde anlık ençok akım	:	**38.1**	**m3/sn**	**11.01.2004**
Gözlem süresinde anlık enaz akım	:	**0.000**	**m3/sn**	**01.10.1987**

Akımlar 01 Ekim 2005 'den 30 Eylül 2006' a kadar m3/sn olarak

Gün	Ekim	Kasım	Aralık	Ocak	Şubat	Mart	Nisan	Mayıs	Haziran	Temmuz	Ağustos	Eylül
01	KURU	KURU	0.003	0.050	0.090	0.390	0.440	0.027	0.003	0.003	KURU	KURU
02	1.10	KURU	0.003	0.050	0.075	0.290	0.390	0.020	0.003	0.003	KURU	KURU
03	0.970	KURU	0.003	0.050	0.050	0.290	0.340	0.013	0.003	0.003	KURU	KURU
04	1.00	KURU	0.003	0.075	0.037	0.290	0.340	0.013	0.003	0.003	KURU	KURU
05	0.050	KURU	0.003	0.075	0.037	0.250	0.340	0.013	0.003	0.003	KURU	KURU
06	0.006	KURU	0.003	0.050	0.110	0.210	0.290	0.013	0.003	0.003	KURU	KURU
07	KURU	KURU	0.003	0.075	0.500	0.250	0.250	0.013	0.003	KURU	KURU	KURU
08	KURU	KURU	0.003	0.075	1.10	1.20	0.210	0.013	0.003	KURU	KURU	KURU
09	KURU	KURU	0.003	0.075	0.570	1.00	0.210	0.013	0.003	KURU	KURU	KURU
10	KURU	KURU	0.003	0.075	0.440	0.640	0.210	0.013	0.003	KURU	KURU	KURU
11	KURU	KURU	0.003	0.075	0.780	0.570	0.210	0.006	0.003	KURU	KURU	KURU
12	KURU	KURU	0.001	0.075	1.10	1.90	0.210	0.006	0.006	KURU	KURU	KURU
13	KURU	KURU	0.003	0.075	0.780	3.76	0.170	0.006	0.006	KURU	KURU	KURU
14	KURU	KURU	0.003	0.075	0.570	4.18	0.210	0.006	0.006	KURU	KURU	KURU
15	KURU	KURU	0.013	0.075	0.440	2.48	0.340	0.006	0.006	KURU	KURU	KURU
16	KURU	KURU	0.003	0.050	0.340	1.75	0.250	0.006	0.006	KURU	KURU	KURU
17	KURU	KURU	0.003	0.075	0.250	1.40	0.210	0.006	0.006	KURU	KURU	KURU
18	KURU	0.050	0.013	0.050	0.290	1.10	0.210	0.006	0.006	KURU	KURU	KURU
19	KURU	0.006	0.110	0.027	0.290	0.970	0.170	0.006	0.006	KURU	KURU	KURU
20	KURU	0.013	0.050	0.037	0.290	0.780	0.135	0.013	0.006	KURU	KURU	KURU
21	KURU	KURU	0.050	0.027	0.290	0.710	0.135	0.006	0.006	KURU	KURU	KURU
22	KURU	KURU	0.050	0.075	0.250	0.710	0.135	0.006	0.006	KURU	KURU	KURU
23	KURU	KURU	0.037	0.075	0.210	0.640	0.135	0.006	0.003	KURU	KURU	KURU
24	KURU	KURU	0.037	0.075	0.210	0.710	0.110	0.006	0.003	KURU	KURU	KURU
25	KURU	KURU	0.027	1.90	0.170	0.710	0.110	0.006	0.003	KURU	KURU	KURU
26	KURU	1.10	0.037	1.10	0.210	0.710	0.090	0.006	0.003	KURU	KURU	KURU
27	KURU	0.006	0.013	0.500	0.210	0.640	0.027	0.006	0.003	KURU	KURU	KURU
28	KURU	0.003	0.020	0.170	0.210	0.570	0.020	0.006	0.006	KURU	KURU	KURU
29	KURU	0.003	0.135	0.110	-----	0.500	0.020	0.006	0.006	KURU	KURU	KURU
30	KURU	0.003	0.110	0.110	-----	0.500	0.020	0.003	0.003	KURU	KURU	KURU
31	KURU	-----	0.090	0.090	-----	0.440	-----	0.003	-----	KURU	KURU	-----
Maks.	1.10	1.10	0.290	1.90	1.90	8.92	0.440	0.050	0.006	0.003	KURU	KURU
Min.	KURU	KURU	0.001	0.027	0.037	0.210	0.020	0.003	0.003	KURU	KURU	KURU
Ortalama	0.101	0.039	0.027	0.177	0.354	0.985	0.198	0.009	0.004	0.001	KURU	KURU
LT/SN/Km2	3.36	1.32	0.901	5.91	11.8	32.8	6.60	0.299	0.143	0.019	0.000	0.000
AKIM mm.	9.00	3.41	2.41	15.8	28.5	88.0	17.1	0.801	0.372	0.052	0.000	0.000
MİL. M3	0.270	0.102	0.072	0.475	0.855	2.64	0.513	0.024	0.011	0.002	0.000	0.000

SU YILI (2006) YILLIK TOPLAM AKIM 4.96 MİLYON M3 165 MM. 5.2 LT/SN/Km2

07. Büyük Menderes Havzasi

D07A099 ALİŞAR DERESİ ALİŞAR

YERİ : **MUĞLA-AYDIN KARAYOLUNUN YAKLAŞIK 20.KM SİNDENDEN SAĞA AYRILAN ALİŞAR YOLUNDAN 2 KM MESAFEDEDİR.**
28°11'30" Doğu - 37°17'56" Kuzey

YAĞIŞ ALANI : **63,00 km2** **YAKLAŞIK KOT : 395 m**

GÖZLEM SÜRESİ : **13.07.1987 - 30.09.2006**

ORTALAMA AKIMLAR : **Gözlem süresinde 0.344 m3/sn. (15 Yıllık) 2006 Su yılında 0.451 m3/sn.**

ANLIK EN ÇOK VE EN AZ AKIMLAR:

2006 Su yılında anlık ençok akım	:	**22.5**	**m3/sn**	**19.12.2005**
2006 Su yılında anlık enaz akım	:	**0.000**	**m3/sn**	**01.10.2005**
Gözlem süresinde anlık ençok akım	:	**30.4**	**m3/sn**	**28.11.1989**
Gözlem süresinde anlık enaz akım	:	**0.000**	**m3/sn**	**08.06.1988**

Akımlar 01 Ekim 2005 'den 30 Eylül 2006' a kadar m3/sn olarak

Gün	Ekim	Kasım	Aralık	Ocak	Şubat	Mart	Nisan	Mayıs	Haziran	Temmuz	Ağustos	Eylül
01	KURU	0.150	0.400	0.250	0.565	1.01	0.565	0.150	0.032	0.052	KURU	KURU
02	8.28	0.150	0.400	0.250	0.400	1.01	0.400	0.180	0.032	0.042	KURU	KURU
03	7.30	0.150	0.400	0.210	0.400	0.919	0.400	0.180	0.032	0.080	KURU	KURU
04	2.99	0.150	0.400	0.210	0.400	0.919	0.400	0.150	0.032	0.150	KURU	KURU
05	1.55	0.150	0.400	0.300	0.400	0.919	0.400	0.180	0.027	0.042	KURU	KURU
06	1.01	0.150	0.400	0.350	0.565	0.919	0.400	0.180	0.032	0.016	KURU	KURU
07	0.565	0.150	0.250	0.300	1.45	1.01	0.400	0.180	0.027	0.008	KURU	KURU
08	0.210	0.150	0.180	0.300	2.38	2.48	0.400	0.150	0.027	0.002	KURU	KURU
09	0.100	0.150	0.150	0.250	1.36	2.07	0.400	0.180	0.027	0.002	KURU	KURU
10	0.120	0.120	0.180	0.250	1.27	1.36	0.400	0.180	0.027	0.002	KURU	KURU
11	0.180	0.120	0.180	0.210	1.86	1.27	0.400	0.180	0.027	0.001	KURU	KURU
12	0.180	0.120	0.180	0.210	2.07	1.86	0.400	0.180	0.027	0.001	KURU	KURU
13	0.180	0.120	0.180	0.180	1.76	5.09	0.400	0.180	0.027	0.001	KURU	KURU
14	0.150	0.120	0.180	0.180	1.36	6.39	0.654	0.180	0.027	KURU	KURU	KURU
15	0.120	0.120	0.250	0.180	1.10	3.50	0.742	0.150	0.027	KURU	KURU	KURU
16	0.100	0.120	0.180	0.180	1.01	2.68	0.654	0.120	0.027	KURU	KURU	KURU
17	0.120	0.120	0.180	0.180	1.01	2.17	0.565	0.080	0.027	KURU	KURU	KURU
18	0.100	0.831	0.300	0.180	1.01	1.76	0.565	0.080	0.027	KURU	KURU	KURU
19	0.100	0.250	7.58	0.180	0.919	1.45	0.400	0.080	0.027	KURU	KURU	KURU
20	0.120	0.300	2.79	0.180	0.919	1.18	0.400	0.068	0.027	KURU	KURU	KURU
21	0.120	0.180	2.27	0.180	0.919	1.10	0.400	0.052	0.027	KURU	KURU	KURU
22	0.120	0.180	2.17	0.180	0.919	0.831	0.400	0.068	0.027	KURU	KURU	KURU
23	0.100	0.180	1.01	0.300	0.831	0.742	0.350	0.068	0.027	KURU	KURU	KURU
24	0.080	0.180	0.180	1.18	0.831	0.742	0.350	0.068	0.027	KURU	KURU	KURU
25	0.100	0.180	0.180	2.79	0.831	0.742	0.250	0.052	0.027	KURU	KURU	0.001
26	0.120	2.27	0.150	1.45	0.831	0.742	0.180	0.052	0.027	KURU	KURU	KURU
27	0.120	0.565	0.150	1.01	0.831	0.742	0.210	0.042	0.068	KURU	KURU	KURU
28	0.120	0.400	0.150	0.742	0.831	0.742	0.250	0.042	0.080	KURU	KURU	0.001
29	0.150	0.400	0.350	0.654	-----	0.742	0.250	0.052	0.068	KURU	KURU	KURU
30	0.150	0.400	0.350	0.565	-----	0.565	0.210	0.068	0.052	KURU	KURU	KURU
31	0.150	-----	0.300	0.565	-----	0.565	-----	0.042	-----	KURU	KURU	-----
Maks.	8.28	6.39	22.5	5.35	3.98	13.5	0.742	0.300	0.350	3.30	KURU	0.002
Min.	KURU	0.120	0.150	0.150	0.400	0.565	0.150	0.042	0.022	KURU	KURU	KURU
Ortalama	0.800	0.288	0.723	0.456	1.04	1.56	0.407	0.117	0.033	0.013	KURU	0.000
LT/SN/Km2	12.7	4.56	11.5	7.24	16.5	24.7	6.45	1.85	0.526	0.204	0.000	0.001
AKIM mm.	34.0	11.8	30.7	19.4	39.8	66.1	16.7	4.96	1.36	0.547	0.000	0.003
MİL. M3	2.14	0.745	1.94	1.22	2.51	4.17	1.05	0.312	0.086	0.034	0.000	0.000

SU YILI (2006) YILLIK TOPLAM AKIM 14.21 MİLYON M3 226 MM. 7.2 LT/SN/Km2

07. Büyük Menderes Havzasi

D07A100 DELİCE DERE KIRIKLAR

YERİ : **MUĞLA-YATAĞAN İLÇESI TURGUT BUCAGINDAN KIRIKLAR MAHALLESINE GIDEN YOLUN 16 KM.SINDEKI KÖPRÜDEDIR.**
28°0'3" Doğu - 37°24'8" Kuzey

YAĞIŞ ALANI : **63,50 km2** **YAKLAŞIK KOT : 336 m**

GÖZLEM SÜRESİ : **13.08.1987 - 30.09.2006**

ORTALAMA AKIMLAR : **Gözlem süresinde 0.349 m3/sn. (19 Yıllık) 2006 Su yılında 0.388 m3/sn.**

ANLIK EN ÇOK VE EN AZ AKIMLAR:

2006 Su yılında anlık ençok akım	:	**44.6**	**m3/sn**	**13.03.2006**
2006 Su yılında anlık enaz akım	:	**0.000**	**m3/sn**	**01.10.2005**
Gözlem süresinde anlık ençok akım	:	**153.**	**m3/sn**	**16.09.2002**
Gözlem süresinde anlık enaz akım	:	**0.000**	**m3/sn**	**01.10.1987**

Akımlar 01 Ekim 2005 'den 30 Eylül 2006' a kadar m3/sn olarak

Gün	Ekim	Kasım	Aralık	Ocak	Şubat	Mart	Nisan	Mayıs	Haziran	Temmuz	Ağustos	Eylül
01	KURU	0.022	0.120	0.356	0.411	0.718	0.411	0.165	0.019	KURU	KURU	KURU
02	1.48	0.022	0.120	0.275	0.411	0.513	0.356	0.165	0.019	KURU	KURU	KURU
03	0.064	0.027	0.083	0.220	0.384	0.462	0.356	0.165	0.019	KURU	KURU	KURU
04	0.027	0.036	0.064	0.193	0.329	0.384	0.513	0.138	0.005	0.064	KURU	KURU
05	0.022	0.027	0.064	0.615	0.329	0.384	0.564	0.120	KURU	0.064	KURU	KURU
06	0.019	0.027	0.064	0.667	3.17	0.329	0.384	0.120	KURU	0.027	KURU	KURU
07	0.016	0.027	0.064	0.615	6.20	0.820	0.302	0.120	KURU	0.019	KURU	KURU
08	0.012	0.027	0.064	0.411	3.59	3.27	0.275	0.101	KURU	0.004	KURU	KURU
09	0.012	0.027	0.064	0.329	1.62	2.35	0.275	0.083	KURU	KURU	KURU	KURU
10	0.012	0.022	0.064	0.275	2.64	1.20	0.247	0.083	KURU	KURU	KURU	KURU
11	0.016	0.022	0.064	0.247	8.60	0.922	0.247	0.064	KURU	KURU	KURU	KURU
12	0.036	0.022	0.064	0.193	5.57	1.20	0.247	0.064	KURU	KURU	KURU	KURU
13	0.027	0.022	0.064	0.165	2.03	5.71	0.247	0.101	KURU	KURU	KURU	KURU
14	0.019	0.022	0.064	0.165	1.34	7.60	0.411	0.064	KURU	KURU	KURU	KURU
15	0.016	0.022	0.871	0.138	1.06	2.35	0.411	0.041	KURU	KURU	KURU	KURU
16	0.016	0.022	0.275	0.138	0.871	1.70	0.275	0.041	KURU	KURU	KURU	KURU
17	0.016	0.027	0.247	0.138	0.922	1.34	0.247	0.041	KURU	KURU	KURU	KURU
18	0.016	0.820	0.356	0.138	1.27	1.78	0.247	0.041	KURU	KURU	KURU	KURU
19	0.016	0.384	5.13	0.462	0.922	1.48	0.220	0.041	KURU	KURU	KURU	KURU
20	0.016	0.564	0.922	1.34	1.06	1.13	0.193	0.041	KURU	KURU	KURU	KURU
21	0.016	0.165	0.513	0.564	0.820	0.922	0.193	0.041	KURU	KURU	KURU	KURU
22	0.016	0.083	0.356	0.384	0.718	0.871	0.193	0.036	KURU	KURU	KURU	KURU
23	0.016	0.083	0.275	1.78	0.615	0.820	0.193	0.032	KURU	KURU	KURU	KURU
24	0.016	0.083	0.220	2.11	0.513	0.769	0.193	0.032	KURU	KURU	KURU	0.004
25	0.016	0.083	0.220	3.59	0.462	0.718	0.165	0.027	KURU	KURU	KURU	0.012
26	0.016	3.48	0.165	1.34	0.513	0.615	0.165	0.022	KURU	KURU	KURU	0.002
27	0.019	0.615	0.138	0.871	0.615	0.564	0.165	0.022	KURU	KURU	KURU	KURU
28	0.019	0.302	0.138	0.667	0.564	0.513	0.165	0.019	KURU	KURU	KURU	KURU
29	0.016	0.193	0.220	0.564	-----	0.462	0.165	0.019	KURU	KURU	KURU	KURU
30	0.016	0.138	0.193	0.411	-----	0.411	0.165	0.019	KURU	KURU	KURU	0.002
31	0.019	-----	0.329	0.411	-----	0.462	-----	0.019	-----	KURU	KURU	-----
Maks.	4.55	11.8	18.8	8.40	35.8	44.6	1.55	0.275	0.019	5.13	KURU	6.00
Min.	KURU	0.022	0.046	0.138	0.329	0.302	0.165	0.019	KURU	KURU	KURU	KURU
Ortalama	0.066	0.247	0.374	0.638	1.70	1.38	0.273	0.067	0.002	0.006	KURU	0.001
LT/SN/Km2	1.04	3.89	5.89	10.0	26.7	21.7	4.30	1.06	0.033	0.090	0.000	0.010
AKIM mm.	2.78	10.1	15.8	26.9	64.7	58.2	11.1	2.84	0.084	0.242	0.000	0.027
MİL. M3	0.177	0.641	1.00	1.71	4.11	3.70	0.708	0.180	0.005	0.015	0.000	0.002

SU YILI (2006) YILLIK TOPLAM AKIM 12.25 MİLYON M3 193 MM. 6.1 LT/SN/Km2

07. Büyük Menderes Havzasi

D07A103 SARIÇAY BAĞARASI

YERİ : **KOÇARLI-SÖKE YOLUNUN YAKLAŞIK 15.KM SİNDEKİ BAĞARASI - ÇALIŞLI KÖYÜ KÖPRÜSÜNDEDİR**

27°34'9" Doğu - 37°42'54" Kuzey

YAĞIŞ ALANI : **212,00 km2** **YAKLAŞIK KOT : 15 m**

GÖZLEM SÜRESİ : **04.05.1988 - 30.09.2006**

ORTALAMA AKIMLAR : **Gözlem süresinde 1.661 m3/sn. (12 Yıllık) 2006 Su yılında 1.672 m3/sn.**

ANLIK EN ÇOK VE EN AZ AKIMLAR:

2006 Su yılında anlık ençok akım	**:**	**168.**	**m3/sn**	**02.10.2005**
2006 Su yılında anlık enaz akım	**:**	**0.000**	**m3/sn**	**10.10.2005**
Gözlem süresinde anlık ençok akım	**:**	**419.**	**m3/sn**	**18.12.2001**
Gözlem süresinde anlık enaz akım	**:**	**0.000**	**m3/sn**	**01.10.1988**

Akımlar 01 Ekim 2005 'den 30 Eylül 2006' a kadar m3/sn olarak

Gün	Ekim	Kasım	Aralık	Ocak	Şubat	Mart	Nisan	Mayıs	Haziran	Temmuz	Ağustos	Eylül
01	KURU	KURU	0.180	3.55	1.39	6.80	0.750	0.250	0.006	0.001	KURU	KURU
02	6.10	KURU	0.080	1.53	1.60	2.68	0.650	0.225	0.003	0.001	KURU	KURU
03	1.86	KURU	0.036	1.04	1.45	1.68	0.615	0.225	0.002	0.001	KURU	KURU
04	1.79	KURU	0.029	0.978	1.39	1.45	0.580	0.200	0.002	0.001	KURU	KURU
05	1.73	KURU	0.025	1.75	1.33	1.21	0.580	0.200	0.002	0.001	KURU	KURU
06	1.66	KURU	0.018	4.23	14.6	1.04	0.615	0.200	0.002	0.001	KURU	KURU
07	1.66	KURU	0.010	3.33	28.7	2.20	0.580	0.200	0.002	0.001	KURU	KURU
08	1.66	KURU	0.010	1.98	14.6	25.2	0.510	0.200	0.002	0.001	KURU	KURU
09	1.60	KURU	0.029	1.27	6.24	11.5	0.440	0.175	0.002	0.001	KURU	KURU
10	0.108	KURU	0.080	1.27	14.8	4.49	0.440	0.150	0.002	KURU	KURU	KURU
11	KURU	KURU	0.120	1.27	44.5	3.11	0.405	0.100	0.002	KURU	KURU	KURU
12	KURU	KURU	0.120	1.27	20.6	2.92	0.370	0.100	0.001	KURU	KURU	KURU
13	KURU	KURU	0.120	1.27	8.24	37.5	0.335	0.100	0.001	KURU	KURU	KURU
14	KURU	KURU	0.120	1.27	5.01	49.2	0.335	0.050	0.001	KURU	KURU	KURU
15	KURU	KURU	0.978	1.27	3.77	10.7	0.370	0.046	0.001	KURU	KURU	KURU
16	KURU	KURU	0.816	1.27	2.92	5.86	0.370	0.042	0.001	KURU	KURU	KURU
17	KURU	KURU	1.75	1.27	2.68	4.48	0.335	0.033	0.001	KURU	KURU	KURU
18	KURU	6.52	1.39	1.27	10.4	4.88	0.300	0.033	0.001	KURU	KURU	KURU
19	KURU	1.21	1.75	5.14	3.99	6.30	0.300	0.029	0.001	KURU	KURU	KURU
20	KURU	4.88	1.90	11.8	3.33	2.89	0.275	0.029	0.001	KURU	KURU	KURU
21	KURU	0.816	1.21	2.76	2.60	2.23	0.275	0.025	0.001	KURU	KURU	KURU
22	KURU	0.120	0.728	1.60	2.13	1.83	0.275	0.025	0.001	KURU	KURU	KURU
23	KURU	0.029	0.596	2.68	1.83	1.51	0.335	0.025	0.001	KURU	KURU	KURU
24	KURU	0.018	0.552	5.82	1.60	1.63	0.545	0.016	0.001	KURU	KURU	KURU
25	KURU	0.390	0.508	17.0	1.45	1.75	0.370	0.016	0.001	KURU	KURU	KURU
26	KURU	38.6	0.390	4.36	1.53	1.27	0.275	0.012	0.001	KURU	KURU	KURU
27	KURU	3.99	0.360	2.44	2.05	1.05	0.250	0.012	0.001	KURU	KURU	KURU
28	KURU	1.21	0.508	1.68	1.53	0.950	0.250	0.008	0.001	KURU	KURU	KURU
29	KURU	0.464	0.596	1.53	-----	0.850	0.250	0.008	0.001	KURU	KURU	KURU
30	KURU	0.300	0.816	1.45	-----	0.850	0.250	0.007	0.001	KURU	KURU	KURU
31	KURU	-----	4.75	1.39	-----	0.850	-----	0.007	-----	KURU	KURU	-----
Maks.	168.	166.	38.6	50.1	120.	121.	0.850	0.250	0.006	0.001	KURU	KURU
Min.	KURU	KURU	0.010	0.978	1.04	0.850	0.250	0.006	0.001	KURU	KURU	KURU
Ortalama	0.586	1.95	0.664	2.93	7.37	6.48	0.408	0.089	0.002	0.000	KURU	KURU
LT/SN/Km2	2.76	9.21	3.13	13.8	34.7	30.6	1.92	0.418	0.007	0.001	0.000	0.000
AKIM mm.	7.40	23.9	8.39	37.0	84.1	81.9	4.98	1.12	0.019	0.004	0.000	0.000
MİL. M3	1.57	5.06	1.78	7.84	17.8	17.4	1.06	0.237	0.004	0.001	0.000	0.000

SU YILI (2006) YILLIK TOPLAM AKIM 52.75 MİLYON M3 249 MM. 7.9 LT/SN/Km2

07. Büyük Menderes Havzasi

D07A106 EMİR ÇAYI. ÇAMBAŞI

YERİ : **KAKLIK-ÇARDAK YOLUNUN 15.KM SİNDEN SAĞA AYRILAN ÇAMBAŞI YOLUNUN 10.KM SİNDEDİR**

29°30'58" Doğu - 37°46'59" Kuzey

YAĞIŞ ALANI : **179,00 km2** **YAKLAŞIK KOT : 690 m**

GÖZLEM SÜRESİ : **01.10.1988 - 30.09.2006**

ORTALAMA AKIMLAR : **Gözlem süresinde 0.291 m3/sn. (6 Yıllık) 2006 Su yılında 0.205 m3/sn.**

ANLIK EN ÇOK VE EN AZ AKIMLAR:

2006 Su yılında anlık ençok akım	:	**2.84**	**m3/sn**	**02.10.2005**
2006 Su yılında anlık enaz akım	:	**0.005**	**m3/sn**	**02.06.2006**
Gözlem süresinde anlık ençok akım	:	**11.2**	**m3/sn**	**22.01.2004**
Gözlem süresinde anlık enaz akım	:	**0.001**	**m3/sn**	**07.08.1991**

Akımlar 01 Ekim 2005 'den 30 Eylül 2006' a kadar m3/sn olarak

Gün	Ekim	Kasım	Aralık	Ocak	Şubat	Mart	Nisan	Mayıs	Haziran	Temmuz	Ağustos	Eylül
01	0.017	0.342	0.266	0.190	0.190	0.722	0.190	0.266	0.007	0.105	0.105	0.105
02	0.494	0.342	0.266	0.190	0.190	0.646	0.190	0.266	0.005	0.105	0.105	0.105
03	0.418	0.342	0.266	0.190	0.190	0.646	0.190	0.266	0.005	0.105	0.105	0.105
04	0.266	0.418	0.266	0.190	0.190	0.646	0.190	0.418	0.005	0.105	0.105	0.105
05	0.190	0.342	0.266	0.190	0.190	0.646	0.190	0.418	0.005	0.105	0.105	0.105
06	0.020	0.342	0.266	0.266	0.190	0.646	0.190	0.418	0.013	0.105	0.105	0.105
07	0.020	0.342	0.266	0.190	0.190	0.646	0.190	0.418	0.105	0.105	0.105	0.105
08	0.020	0.342	0.266	0.190	0.190	0.646	0.190	0.266	0.105	0.105	0.105	0.105
09	0.020	0.342	0.266	0.190	0.190	0.646	0.190	0.105	0.105	0.105	0.105	0.105
10	0.020	0.342	0.266	0.190	0.190	0.646	0.190	0.105	0.105	0.105	0.020	0.105
11	0.020	0.342	0.266	0.190	0.418	0.646	0.190	0.105	0.105	0.105	0.020	0.105
12	0.105	0.342	0.266	0.190	0.874	0.646	0.190	0.105	0.190	0.105	0.020	0.105
13	0.105	0.418	0.266	0.190	0.646	0.950	0.190	0.020	0.105	0.105	0.020	0.105
14	0.105	0.418	0.266	0.190	0.494	1.48	0.190	0.020	0.105	0.105	0.020	0.105
15	0.105	0.418	0.266	0.190	0.418	1.06	0.190	0.020	0.020	0.105	0.020	0.105
16	0.105	0.418	0.266	0.190	0.418	0.722	0.190	0.190	0.020	0.105	0.020	0.105
17	0.105	0.418	0.266	0.190	0.418	0.418	0.190	0.020	0.020	0.105	0.020	0.105
18	0.105	0.494	0.266	0.190	0.418	0.342	0.190	0.105	0.020	0.105	0.020	0.105
19	0.105	0.494	0.494	0.190	0.418	0.342	0.190	0.105	0.020	0.105	0.020	0.105
20	0.105	0.494	0.418	0.190	0.418	0.342	0.190	0.105	0.020	0.105	0.020	0.105
21	0.105	0.342	0.266	0.190	0.418	0.342	0.190	0.105	0.020	0.105	0.020	0.105
22	0.190	0.342	0.190	0.190	0.418	0.266	0.190	0.105	0.020	0.105	0.020	0.105
23	0.190	0.342	0.190	0.190	0.418	0.105	0.190	0.105	0.020	0.105	0.020	0.105
24	0.190	0.266	0.190	0.190	0.418	0.190	0.190	0.020	0.020	0.105	0.020	0.105
25	0.105	0.266	0.190	0.266	0.418	0.266	0.190	0.013	0.020	0.105	0.020	0.105
26	0.190	0.266	0.190	0.266	0.418	0.190	0.190	0.010	0.020	0.105	0.020	0.105
27	0.190	0.266	0.190	0.266	0.874	0.190	0.190	0.008	0.020	0.105	0.020	0.105
28	0.190	0.266	0.190	0.190	0.722	0.190	0.190	0.008	0.020	0.105	0.020	0.105
29	0.190	0.266	0.190	0.190	-----	0.190	0.190	0.007	0.020	0.105	0.020	0.105
30	0.190	0.266	0.190	0.190	-----	0.190	0.190	0.007	0.020	0.105	0.105	0.105
31	0.266	-----	0.190	0.190	-----	0.190	-----	0.007	-----	0.105	0.105	-----
Maks.	2.84	0.950	0.646	0.266	0.950	2.00	0.494	1.27	0.266	0.105	0.105	0.105
Min.	0.017	0.266	0.190	0.190	0.190	0.105	0.105	0.007	0.005	0.105	0.020	0.105
Ortalama	0.143	0.355	0.254	0.200	0.391	0.509	0.190	0.133	0.043	0.105	0.050	0.105
LT/SN/Km2	0.801	1.98	1.42	1.12	2.18	2.85	1.06	0.745	0.239	0.587	0.280	0.587
AKIM mm.	2.15	5.14	3.80	2.99	5.28	7.62	2.75	2.00	0.620	1.57	0.751	1.52
MİL. M3	0.384	0.919	0.680	0.535	0.946	1.36	0.492	0.357	0.111	0.281	0.134	0.272

SU YILI (2006) YILLIK TOPLAM AKIM 6.47 MİLYON M3 36 MM. 1.1 LT/SN/Km2

07. Büyük Menderes Havzasi

D07A115 BÜYÜK MENDERES N. YENİCE REGÜLATÖR GİRİŞİ

YERİ : **YENİCE REG-CİNDERE BRJ.GİDEN YOLUN 5.KM SİNDEDİR.**
28°58'11" Doğu - 38°3'7" Kuzey

YAĞIŞ ALANI : **11852,00 km2** **YAKLAŞIK KOT : 160 m**

GÖZLEM SÜRESİ : **01.10.2004 - 30.09.2006**

ORTALAMA AKIMLAR : **Gözlem süresinde 18.084 m3/sn. (2 Yıllık) 2006 Su yılında 15.703 m3/sn.**

ANLIK EN ÇOK VE EN AZ AKIMLAR:

2006 Su yılında anlık ençok akım	:	**62.0**	**m3/sn**	**03.07.2006**
2006 Su yılında anlık enaz akım	:	**0.202**	**m3/sn**	**28.11.2005**
Gözlem süresinde anlık ençok akım	:	**64.2**	**m3/sn**	**15.07.2005**
Gözlem süresinde anlık enaz akım	:	**0.202**	**m3/sn**	**28.11.2005**

Akımlar 01 Ekim 2005 'den 30 Eylül 2006' a kadar m3/sn olarak

Gün	Ekim	Kasım	Aralık	Ocak	Şubat	Mart	Nisan	Mayıs	Haziran	Temmuz	Ağustos	Eylül
01	15.9	1.70	0.440	0.818	1.07	0.944	0.692	23.2	20.4	55.0	54.0	43.5
02	13.2	1.32	1.57	0.818	0.944	1.07	0.692	21.6	18.6	49.0	54.0	43.5
03	3.40	1.32	1.57	0.818	0.818	0.944	0.692	19.3	18.3	57.0	42.5	43.5
04	2.38	1.32	1.57	0.944	0.818	0.944	0.692	17.9	19.0	53.5	54.5	46.5
05	2.38	1.32	1.70	0.944	0.818	0.944	0.818	3.06	21.6	39.0	54.0	42.5
06	2.38	1.20	1.70	0.944	0.818	0.944	0.818	1.87	24.4	39.5	54.0	37.0
07	2.21	1.20	1.70	0.944	0.944	0.944	0.818	1.57	29.0	41.5	53.5	37.0
08	2.21	1.20	1.70	0.944	0.944	1.07	0.692	1.32	30.5	42.0	53.5	37.0
09	2.21	1.20	1.70	0.944	0.944	1.20	0.818	1.20	39.0	42.5	53.5	37.5
10	2.21	1.20	1.87	0.944	0.944	1.07	0.818	7.48	32.5	43.0	52.0	37.5
11	2.21	1.20	1.70	0.944	0.944	1.07	0.818	12.4	33.0	43.0	47.0	37.5
12	2.21	1.20	1.87	0.944	1.07	1.07	0.818	13.2	32.0	43.0	37.0	37.5
13	2.21	1.20	1.87	0.944	1.07	1.20	0.818	12.7	32.0	47.0	49.5	37.5
14	2.21	1.20	1.70	0.944	1.07	2.04	0.818	13.2	17.6	51.5	48.0	34.0
15	2.21	1.20	1.70	0.944	0.818	1.70	1.07	13.2	17.6	52.5	43.5	28.5
16	2.21	1.20	1.45	0.944	0.818	1.20	1.07	13.8	21.6	52.5	46.0	28.0
17	2.04	1.20	1.45	0.944	0.818	1.20	1.07	13.5	20.8	52.5	46.5	28.0
18	2.04	1.20	1.45	0.944	0.818	1.20	0.944	14.1	20.4	52.5	46.5	27.2
19	2.04	1.20	1.70	0.944	0.818	1.20	0.944	13.8	23.2	52.5	47.0	23.2
20	1.57	1.20	1.57	1.07	0.818	1.20	8.00	13.8	32.5	52.5	47.5	19.0
21	1.20	1.20	1.32	1.07	0.818	1.20	13.5	13.8	39.5	53.5	48.0	16.5
22	1.20	1.20	1.20	1.07	0.818	0.944	16.2	12.9	40.0	53.0	45.0	11.5
23	1.20	1.20	1.07	1.07	0.818	0.818	18.3	13.2	44.5	53.0	40.5	11.0
24	1.20	1.20	1.20	1.07	0.818	0.818	18.3	14.1	50.5	53.5	41.0	11.0
25	1.20	1.20	1.20	1.20	0.818	2.89	18.6	14.7	51.0	54.0	42.5	9.35
26	1.20	2.21	1.20	7.74	0.818	1.20	19.7	20.8	51.0	54.0	43.0	0.440
27	1.20	1.57	1.20	8.81	0.944	1.07	22.8	24.0	50.5	53.0	43.5	0.270
28	9.35	0.406	1.07	8.00	0.944	0.818	23.6	24.0	50.0	53.0	43.5	0.236
29	12.9	0.202	0.944	2.89	-----	0.818	23.6	20.8	50.0	53.5	43.5	0.236
30	12.9	0.202	0.944	1.20	-----	0.818	23.6	20.4	52.5	53.5	43.5	0.236
31	10.7	-----	0.818	1.07	-----	0.692	-----	20.4	-----	53.5	43.5	-----
Maks.	16.5	3.23	1.87	28.0	1.07	5.40	23.6	24.0	58.0	62.0	54.5	50.5
Min.	1.20	0.202	0.236	0.692	0.818	0.692	0.692	1.20	15.6	14.7	6.96	0.236
Ortalama	3.99	1.19	1.42	1.74	0.890	1.14	7.40	13.9	32.8	50.0	47.1	25.6
LT/SN/Km2	0.337	0.100	0.120	0.146	0.075	0.096	0.625	1.17	2.77	4.22	3.98	2.16
AKIM mm.	0.902	0.259	0.322	0.392	0.182	0.257	1.62	3.14	7.17	11.3	10.7	5.59
MİL. M3	10.7	3.07	3.81	4.65	2.15	3.04	19.2	37.3	85.0	134.	126.	66.2

SU YILI (2006) YILLIK TOPLAM AKIM 495.12 MİLYON M3 42 MM. 1.3 LT/SN/Km2

07. Büyük Menderes Havzasi

D07A120 ÇAPALI GÖLÜ ÇIKIŞ

YERİ : **ISPARTA DİNAR KARAYOLUNU TAKİBEN KARAKUYU KÖYÜNE VARILIR. KARAKUYU TİREN İST.DAN 500M İLERDE KANAL ÜZERİNDEDİR. HARİTA PAFTA NO: L24-D3**
30°12'16" Doğu - 38°4'34" Kuzey

YAĞIŞ ALANI : **368,90 km2** **YAKLAŞIK KOT : 1005 m**

GÖZLEM SÜRESİ : **01.10.2004 - 30.09.2006**

ORTALAMA AKIMLAR : **Gözlem süresinde 0.949 m3/sn. (2 Yıllık) 2006 Su yılında 0.598 m3/sn.**

ANLIK EN ÇOK VE EN AZ AKIMLAR:

2006 Su yılında anlık ençok akım	**:**	**0.896 m3/sn**	**26.04.2006**
2006 Su yılında anlık enaz akım	**:**	**0.072 m3/sn**	**30.09.2006**
Gözlem süresinde anlık ençok akım	**:**	**2.75 m3/sn**	**19.08.2005**
Gözlem süresinde anlık enaz akım	**:**	**0.000 m3/sn**	**29.10.2004**

Akımlar 01 Ekim 2005 'den 30 Eylül 2006' a kadar m3/sn olarak

Gün	Ekim	Kasım	Aralık	Ocak	Şubat	Mart	Nisan	Mayıs	Haziran	Temmuz	Ağustos	Eylül
01	0.576	0.676	0.698	0.593	0.273	0.720	0.830	0.187	0.560	0.600	0.600	0.410
02	0.676	0.676	0.676	0.610	0.284	0.742	0.830	0.187	0.560	0.600	0.580	0.410
03	0.764	0.676	0.676	0.610	0.720	0.764	0.830	0.187	0.560	0.580	0.560	0.410
04	0.676	0.676	0.654	0.610	0.720	0.786	0.830	0.187	0.560	0.600	0.520	0.410
05	0.676	0.676	0.654	0.593	0.720	0.786	0.874	0.540	0.560	0.600	0.520	0.425
06	0.676	0.676	0.654	0.576	0.742	0.786	0.874	0.540	0.560	0.600	0.410	0.425
07	0.676	0.676	0.654	0.133	0.742	0.786	0.874	0.540	0.600	0.600	0.410	0.425
08	0.676	0.676	0.632	0.090	0.742	0.786	0.896	0.540	0.600	0.560	0.540	0.410
09	0.676	0.676	0.632	0.090	0.742	0.786	0.830	0.540	0.600	0.560	0.480	0.410
10	0.676	0.676	0.632	0.090	0.742	0.786	0.830	0.540	0.600	0.560	0.395	0.410
11	0.676	0.654	0.632	0.090	0.742	0.786	0.830	0.540	0.600	0.540	0.395	0.410
12	0.676	0.654	0.632	0.090	0.742	0.786	0.830	0.540	0.620	0.540	0.425	0.410
13	0.676	0.632	0.610	0.090	0.742	0.786	0.852	0.540	0.620	0.540	0.560	0.410
14	0.676	0.632	0.610	0.090	0.742	0.786	0.852	0.540	0.620	0.540	0.560	0.410
15	0.676	0.632	0.610	0.090	0.742	0.808	0.874	0.540	0.620	0.540	0.520	0.410
16	0.676	0.610	0.654	0.090	0.742	0.830	0.830	0.540	0.600	0.540	0.500	0.395
17	0.676	0.610	0.676	0.090	0.742	0.830	0.852	0.540	0.600	0.540	0.500	0.395
18	0.676	0.610	0.676	0.090	0.742	0.830	0.830	0.540	0.600	0.540	0.480	0.395
19	0.676	0.632	0.632	0.090	0.742	0.830	0.830	0.540	0.600	0.520	0.480	0.395
20	0.676	0.654	0.720	0.720	0.742	0.830	0.852	0.540	0.600	0.520	0.480	0.380
21	0.676	0.764	0.720	0.720	0.742	0.830	0.874	0.540	0.600	0.480	0.480	0.425
22	0.676	0.786	0.676	0.720	0.742	0.830	0.896	0.540	0.600	0.480	0.460	0.460
23	0.676	0.786	0.654	0.720	0.742	0.830	0.874	0.540	0.600	0.460	0.440	0.425
24	0.676	0.764	0.654	0.720	0.742	0.830	0.852	0.540	0.600	0.460	0.440	0.350
25	0.676	0.742	0.632	0.720	0.742	0.852	0.874	0.540	0.600	0.460	0.460	0.500
26	0.676	0.720	0.610	0.720	0.742	0.852	0.896	0.540	0.600	0.410	0.440	0.770
27	0.676	0.720	0.593	0.720	0.720	0.852	0.874	0.540	0.600	0.410	0.440	0.209
28	0.676	0.720	0.593	0.720	0.720	0.852	0.896	0.540	0.600	0.500	0.440	0.146
29	0.676	0.698	0.593	0.167	-----	0.852	0.187	0.540	0.600	0.500	0.425	0.110
30	0.676	0.698	0.610	0.090	-----	0.830	0.187	0.560	0.600	0.600	0.425	0.072
31	0.676	-----	0.632	0.090	-----	0.830	-----	0.560	-----	0.600	0.410	-----
Maks.	0.764	0.786	0.720	0.720	0.742	0.852	0.896	0.560	0.620	0.600	0.600	0.770
Min.	0.576	0.610	0.593	0.090	0.167	0.720	0.103	0.187	0.520	0.410	0.395	0.072
Ortalama	0.676	0.683	0.645	0.375	0.705	0.809	0.811	0.496	0.595	0.535	0.477	0.387
LT/SN/Km2	1.83	1.85	1.75	1.02	1.91	2.19	2.20	1.34	1.61	1.45	1.29	1.05
AKIM mm.	4.91	4.80	4.68	2.72	4.62	5.87	5.70	3.60	4.18	3.88	3.46	2.72
MİL. M3	1.81	1.77	1.73	1.01	1.71	2.17	2.10	1.33	1.54	1.43	1.28	1.00

SU YILI (2006) YILLIK TOPLAM AKIM 18.88 MİLYON M3 51 MM. 1.6 LT/SN/Km2

07. Büyük Menderes Havzasi

D07A121 KAYRAN DERESİ. PAMUKÖREN

YERİ : **AYDIN-DENIZLI KARAYOLUNUN 70.KM SİNDEN SOLA AYRILAN PAMUKÖREN YOLUNUN 5.KM SİNDEDIR**

28°31'37" Doğu - 37°55'51" Kuzey

YAĞIŞ ALANI : **55,20 km2** **YAKLAŞIK KOT : 249 m**

GÖZLEM SÜRESİ : **24.01.2001 - 30.09.2006**

ORTALAMA AKIMLAR : **Gözlem süresinde 0.121 m3/sn. (4 Yıllık) 2006 Su yılında 0.129 m3/sn.**

ANLIK EN ÇOK VE EN AZ AKIMLAR:

2006 Su yılında anlık ençok akım	:	**7.60**	**m3/sn**	**11.02.2006**
2006 Su yılında anlık enaz akım	:	**0.000**	**m3/sn**	**01.10.2005**
Gözlem süresinde anlık ençok akım	:	**18.6**	**m3/sn**	**25.12.2001**
Gözlem süresinde anlık enaz akım	:	**0.000**	**m3/sn**	**01.10.2001**

Akımlar 01 Ekim 2005 'den 30 Eylül 2006' a kadar m3/sn olarak

Gün	Ekim	Kasım	Aralık	Ocak	Şubat	Mart	Nisan	Mayıs	Haziran	Temmuz	Ağustos	Eylül
01	KURU	KURU	KURU	KURU	0.036	0.654	0.108	KURU	KURU	KURU	KURU	KURU
02	0.078	KURU	KURU	KURU	0.030	0.518	0.108	KURU	KURU	KURU	KURU	KURU
03	0.054	KURU	KURU	KURU	0.036	0.602	0.108	KURU	KURU	KURU	KURU	KURU
04	0.009	KURU	KURU	KURU	0.036	0.560	0.108	KURU	KURU	KURU	KURU	KURU
05	0.005	KURU	KURU	KURU	0.036	0.464	0.108	0.009	KURU	KURU	KURU	KURU
06	0.005	KURU	KURU	KURU	0.315	0.386	0.108	0.009	KURU	KURU	KURU	KURU
07	0.005	KURU	KURU	KURU	0.630	0.360	0.108	0.025	KURU	KURU	KURU	KURU
08	0.005	KURU	KURU	KURU	0.630	0.903	0.108	0.025	KURU	KURU	KURU	KURU
09	0.005	KURU	KURU	KURU	0.373	0.822	0.108	0.018	KURU	KURU	KURU	KURU
10	0.003	KURU	KURU	KURU	0.630	0.726	0.108	0.009	KURU	KURU	KURU	KURU
11	0.003	KURU	KURU	KURU	4.48	0.726	0.096	KURU	KURU	KURU	KURU	KURU
12	0.003	KURU	KURU	KURU	3.92	0.726	0.114	KURU	KURU	KURU	KURU	KURU
13	0.009	KURU	KURU	KURU	1.17	0.798	0.096	KURU	KURU	KURU	KURU	KURU
14	0.009	KURU	KURU	KURU	0.750	1.75	0.108	KURU	KURU	KURU	KURU	KURU
15	0.012	KURU	KURU	KURU	0.616	1.17	0.160	KURU	KURU	KURU	KURU	KURU
16	0.012	KURU	KURU	KURU	0.464	1.10	0.108	KURU	KURU	KURU	KURU	KURU
17	0.018	KURU	KURU	KURU	0.518	1.04	0.084	KURU	KURU	KURU	KURU	KURU
18	0.025	0.009	KURU	KURU	0.750	0.969	0.084	KURU	KURU	KURU	KURU	KURU
19	0.025	0.018	0.574	0.230	0.654	0.903	0.072	KURU	KURU	KURU	KURU	KURU
20	0.025	0.030	0.220	0.546	0.616	0.870	0.072	KURU	KURU	KURU	KURU	KURU
21	0.025	0.018	0.060	0.288	0.574	0.798	0.072	KURU	KURU	KURU	KURU	KURU
22	0.030	KURU	0.005	0.042	0.504	0.574	0.072	KURU	KURU	KURU	KURU	KURU
23	0.030	KURU	KURU	0.042	0.438	0.412	0.140	KURU	KURU	KURU	KURU	KURU
24	0.018	KURU	KURU	0.003	0.373	0.351	0.120	KURU	KURU	KURU	KURU	KURU
25	0.009	KURU	KURU	0.654	0.351	0.306	0.025	KURU	KURU	KURU	KURU	KURU
26	KURU	0.386	KURU	0.270	0.425	0.260	0.003	KURU	KURU	KURU	KURU	KURU
27	KURU	0.078	KURU	0.230	0.451	0.210	KURU	KURU	KURU	KURU	KURU	KURU
28	KURU	KURU	KURU	0.210	0.412	0.150	KURU	KURU	KURU	KURU	KURU	KURU
29	KURU	KURU	KURU	0.160	-----	0.108	KURU	KURU	KURU	KURU	KURU	KURU
30	KURU	KURU	KURU	0.108	-----	0.108	KURU	KURU	KURU	KURU	KURU	KURU
31	KURU	-----	KURU	0.096	-----	0.108	-----	KURU	-----	KURU	KURU	-----
Maks.	0.702	4.10	4.67	6.00	7.60	4.29	0.399	0.048	KURU	0.002	0.001	0.002
Min.	KURU	KURU	KURU	KURU	0.005	0.108	KURU	KURU	KURU	KURU	KURU	KURU
Ortalama	0.014	0.018	0.028	0.093	0.722	0.627	0.084	0.003	KURU	KURU	KURU	KURU
LT/SN/Km2	0.247	0.325	0.502	1.68	13.1	11.4	1.51	0.056	0.000	0.000	0.000	0.000
AKIM mm.	0.661	0.844	1.34	4.51	31.6	30.4	3.92	0.149	0.000	0.000	0.000	0.000
MİL. M3	0.036	0.047	0.074	0.249	1.75	1.68	0.217	0.008	0.000	0.000	0.000	0.000

SU YILI (2006) YILLIK TOPLAM AKIM 4.06 MİLYON M3 74 MM. 2.3 LT/SN/Km2

07. Büyük Menderes Havzasi

D07A122 BANAZ Ç. BANAZ

YERİ : **BANAZ İLÇESİ BANAZ KÖYÜNDEN İTİBAREN 2KM SONRA DERE ÜZERİNDEDİR.(PAFTA K23)**
29°44'1" Doğu - 38°47'9" Kuzey

YAĞIŞ ALANI : **139,64 km2** **YAKLAŞIK KOT : 958 m**

GÖZLEM SÜRESİ : **01.01.2005 - 30.09.2006**

ORTALAMA AKIMLAR : **Gözlem süresinde 0.811 m3/sn. (1 Yıllık) 2006 Su yılında 0.811 m3/sn.**

ANLIK EN ÇOK VE EN AZ AKIMLAR:

2006 Su yılında anlık ençok akım	:	**13.9**	**m3/sn**	**11.02.2006**
2006 Su yılında anlık enaz akım	:	**0.012**	**m3/sn**	**10.09.2006**
Gözlem süresinde anlık ençok akım	:	**13.9**	**m3/sn**	**11.02.2006**
Gözlem süresinde anlık enaz akım	:	**0.012**	**m3/sn**	**10.09.2006**

8. Anahtar Eğrisi (Seviyeler cm olarak)

Seviye	Akım	Seviye	Akım	Seviye	Akım	Seviye	Akım
1	0.011	15	0.620	70	7.8	120	16.3
3	0.052	25	1.5	80	9.3	130	18.0
5	0.105	40	3.2	90	11.2	140	20.0
7	0.178	50	4.7	100	12.8	150	22.0
9	0.260	60	6.3	110	14.5	160	24.5

Akımlar 01 Ekim 2005 'den 30 Eylül 2006' a kadar m3/sn olarak

Gün	Ekim	Kasım	Aralık	Ocak	Şubat	Mart	Nisan	Mayıs	Haziran	Temmuz	Ağustos	Eylül
01	0.112	0.352	0.412	0.513	0.513	2.00	1.77	1.53	0.664	0.322	0.150	0.021
02	0.172	0.352	0.412	0.412	0.513	1.50	1.77	1.53	0.664	0.270	0.150	0.021
03	0.172	0.352	0.412	0.412	0.513	3.50	1.77	1.53	0.664	0.374	0.150	0.021
04	0.172	0.352	0.412	0.412	0.513	1.67	1.89	1.41	0.664	0.374	0.150	0.021
05	0.172	0.352	0.412	0.918	0.513	1.27	1.77	1.41	0.664	0.374	0.150	0.016
06	0.172	0.352	0.412	0.817	1.15	0.918	1.65	1.41	0.597	0.374	0.150	0.016
07	0.112	0.232	0.412	0.614	1.38	0.918	1.65	1.41	0.664	0.374	0.112	0.016
08	0.112	0.352	0.412	0.614	0.918	2.66	1.65	1.41	0.597	0.374	0.112	0.016
09	0.112	0.352	0.292	0.614	0.918	1.67	1.65	1.41	0.597	0.374	0.112	0.012
10	0.112	0.352	0.352	0.614	1.27	1.15	1.65	1.41	0.597	0.322	0.112	0.012
11	0.112	0.352	0.352	0.513	9.53	1.15	1.65	1.29	0.664	0.270	0.112	0.150
12	0.112	0.352	0.352	0.412	5.05	1.15	1.65	1.21	0.664	0.230	0.074	0.074
13	0.112	0.352	0.352	0.412	2.16	1.15	1.65	1.21	0.664	0.230	0.074	0.074
14	0.112	0.352	0.352	0.412	2.00	7.23	1.65	1.21	0.664	0.322	0.074	0.074
15	0.112	0.352	0.352	0.412	2.00	4.90	1.77	1.12	0.664	0.270	0.074	0.074
16	0.112	0.352	0.352	0.412	2.00	3.83	1.65	1.12	0.664	0.270	0.059	0.112
17	0.172	0.352	0.412	0.412	1.83	3.38	1.65	1.12	0.664	0.230	0.059	0.112
18	0.172	0.352	0.412	0.412	2.00	3.08	1.65	1.12	0.597	0.270	0.044	0.112
19	0.172	0.352	1.27	2.00	2.00	2.93	1.65	1.12	0.478	0.230	0.044	0.112
20	0.172	0.716	0.716	2.83	3.17	2.78	1.65	1.12	0.478	0.230	0.044	0.112
21	0.112	0.513	0.412	1.38	2.66	2.48	1.65	1.12	0.426	0.190	0.044	0.150
22	0.172	0.412	0.412	1.15	2.33	2.36	1.77	1.12	0.426	0.230	0.035	0.150
23	0.172	0.352	0.352	1.03	2.00	2.24	1.53	0.950	0.374	0.190	0.035	0.150
24	0.172	0.352	0.352	1.03	2.00	2.12	1.53	0.731	0.374	0.190	0.035	0.150
25	0.172	0.412	0.352	0.716	1.83	2.12	1.53	0.731	0.374	0.150	0.035	0.150
26	0.172	1.15	0.352	0.716	2.00	2.00	1.53	0.798	0.374	0.150	0.035	0.270
27	0.172	0.716	0.352	0.614	2.00	1.89	1.53	0.798	0.322	0.150	0.035	0.270
28	0.172	0.614	0.352	0.614	1.67	1.89	1.53	0.664	0.190	0.190	0.035	0.270
29	0.232	0.513	0.513	0.513	-----	1.89	1.53	0.664	0.230	0.150	0.028	0.270
30	0.352	0.412	0.412	0.513	-----	1.89	1.53	0.664	0.322	0.150	0.028	0.270
31	0.352	-----	0.513	0.513	-----	1.89	-----	0.664	-----	0.150	0.028	-----
Maks.	0.352	1.83	4.84	11.2	13.9	11.7	2.24	1.53	0.664	0.478	0.150	0.270
Min.	0.112	0.232	0.292	0.412	0.513	0.918	1.53	0.664	0.059	0.150	0.028	0.012
Ortalama	0.162	0.424	0.427	0.741	2.02	2.31	1.65	1.13	0.533	0.257	0.077	0.109
LT/SN/Km2	1.16	3.04	3.06	5.30	14.4	16.5	11.8	8.09	3.82	1.84	0.550	0.782
AKIM mm.	3.11	7.88	8.19	14.2	34.9	44.3	30.6	21.7	9.89	4.93	1.47	2.03
MİL. M3	0.435	1.10	1.14	1.98	4.88	6.19	4.28	3.02	1.38	0.689	0.206	0.283

SU YILI (2006) YILLIK TOPLAM AKIM 25.58 MİLYON M3 183 MM. 5.8 LT/SN/Km2

07. Büyük Menderes Havzasi

D07A124 AVŞAR ÇAYI HAYDARLI

YERİ : ISPARTA-DİNAR-HAYDARLI DEVLET YOLUNU TAKİBEN HAYDARLI KASABASINA VARILIR. KASABANIN KUZEY BATISINDA BULUNAN AVŞAR ÇAYINI TAKİBEN, TAKRİBEN 7 KM SONRA DERENİN SAĞ SAHİLİNDEDİR. 30°23'8" Doğu - 38°18'33" Kuzey

YAĞIŞ ALANI : 18,00 km2 **YAKLAŞIK KOT :** 1316 m

GÖZLEM SÜRESİ : 20.09.2005 - 30.09.2006

ORTALAMA AKIMLAR : Gözlem süresinde 0.119 m3/sn. (1 Yıllık) 2006 Su yılında 0.119 m3/sn.

ANLIK EN ÇOK VE EN AZ AKIMLAR:

2006 Su yılında anlık ençok akım	:	1.02	m3/sn	08.04.2006
2006 Su yılında anlık enaz akım	:	0.004	m3/sn	27.07.2006
Gözlem süresinde anlık ençok akım	:	1.02	m3/sn	08.04.2006
Gözlem süresinde anlık enaz akım	:	0.003	m3/sn	27.07.2004

1. Anahtar Eğrisi (Seviyeler cm olarak)

Seviye	Akım	Seviye	Akım	Seviye	Akım	Seviye	Akım
6	0.001	16	0.063	25	0.269	50	2.0
9	0.007	17	0.077	30	0.468	60	3.3
11	0.016	18	0.092	35	0.740	70	5.0
13	0.030	19	0.110	40	1.1	80	7.3
15	0.050	20	0.133	45	1.5	90	9.9

Akımlar 01 Ekim 2005 'den 30 Eylül 2006' a kadar m3/sn olarak

Gün	Ekim	Kasım	Aralık	Ocak	Şubat	Mart	Nisan	Mayıs	Haziran	Temmuz	Ağustos	Eylül
01	0.110	0.050	0.030	0.030	0.030	0.092	0.740	0.133	0.022	0.016	0.004	0.004
02	0.187	0.050	0.016	0.030	0.030	0.110	0.810	0.110	0.022	0.016	0.004	0.004
03	0.160	0.050	0.016	0.030	0.030	0.577	0.686	0.133	0.022	0.016	0.004	0.004
04	0.133	0.050	0.011	0.030	0.030	0.522	0.522	0.160	0.022	0.011	0.004	0.004
05	0.110	0.063	0.011	0.030	0.030	0.522	0.468	0.215	0.022	0.011	0.004	0.004
06	0.092	0.063	0.011	0.030	0.030	0.522	0.468	0.215	0.022	0.011	0.004	0.004
07	0.077	0.063	0.016	0.030	0.030	0.522	0.686	0.187	0.022	0.011	0.004	0.007
08	0.063	0.063	0.016	0.030	0.030	0.522	1.02	0.160	0.022	0.011	0.004	0.007
09	0.050	0.050	0.011	0.030	0.030	0.522	0.740	0.160	0.022	0.011	0.004	0.007
10	0.092	0.050	0.011	0.030	0.030	0.522	0.740	0.160	0.022	0.011	0.004	0.007
11	0.092	0.050	0.011	0.030	0.039	0.468	0.740	0.160	0.022	0.011	0.004	0.007
12	0.077	0.050	0.016	0.030	0.039	0.468	0.740	0.160	0.022	0.011	0.004	0.007
13	0.077	0.050	0.016	0.030	0.039	0.468	0.686	0.160	0.022	0.011	0.004	0.007
14	0.077	0.050	0.011	0.030	0.039	0.468	0.810	0.110	0.022	0.007	0.004	0.011
15	0.077	0.050	0.016	0.030	0.039	0.468	0.740	0.077	0.016	0.007	0.004	0.011
16	0.063	0.050	0.011	0.030	0.039	0.468	0.686	0.050	0.016	0.007	0.004	0.011
17	0.050	0.050	0.011	0.030	0.039	0.468	0.686	0.030	0.016	0.007	0.004	0.011
18	0.050	0.050	0.050	0.030	0.039	0.468	0.686	0.030	0.016	0.007	0.004	0.011
19	0.050	0.063	0.039	0.030	0.039	0.468	0.631	0.030	0.016	0.007	0.004	0.011
20	0.039	0.077	0.039	0.030	0.039	0.468	0.522	0.022	0.016	0.007	0.004	0.011
21	0.022	0.050	0.039	0.030	0.039	0.522	0.428	0.022	0.016	0.007	0.004	0.011
22	0.030	0.050	0.039	0.030	0.050	0.686	0.428	0.022	0.016	0.007	0.004	0.011
23	0.030	0.050	0.039	0.030	0.050	0.950	0.309	0.022	0.016	0.007	0.004	0.016
24	0.030	0.050	0.039	0.030	0.077	0.740	0.215	0.022	0.016	0.007	0.004	0.016
25	0.030	0.050	0.039	0.030	0.110	0.577	0.215	0.022	0.016	0.007	0.004	0.016
26	0.030	0.050	0.039	0.030	0.110	0.577	0.215	0.022	0.016	0.007	0.004	0.016
27	0.039	0.050	0.039	0.030	0.092	0.577	0.215	0.022	0.016	0.004	0.004	0.016
28	0.039	0.050	0.039	0.030	0.077	0.522	0.187	0.022	0.016	0.004	0.004	0.016
29	0.039	0.050	0.050	0.030	-----	0.522	0.133	0.022	0.016	0.004	0.004	0.016
30	0.050	0.039	0.050	0.030	-----	0.740	0.133	0.022	0.016	0.004	0.004	0.016
31	0.050	-----	0.050	0.030	-----	0.740	-----	0.022	-----	0.004	0.004	-----
Maks.	0.187	0.077	0.050	0.030	0.110	0.950	1.02	0.215	0.022	0.022	0.004	0.016
Min.	0.022	0.039	0.011	0.030	0.030	0.092	0.133	0.022	0.016	0.004	0.004	0.004
Ortalama	0.068	0.053	0.027	0.030	0.046	0.525	0.543	0.087	0.019	0.009	0.004	0.010
LT/SN/Km2	3.79	2.93	1.49	1.67	2.57	29.2	30.2	4.85	1.04	0.482	0.222	0.556
AKIM mm.	10.2	7.59	3.99	4.46	6.22	78.1	78.2	13.0	2.71	1.29	0.595	1.44
MİL. M3	0.183	0.137	0.072	0.080	0.112	1.41	1.41	0.234	0.049	0.023	0.011	0.026

SU YILI (2006) YILLIK TOPLAM AKIM 3.75 MİLYON M3 208 MM. 6.6 LT/SN/Km2

08

BATI AKDENİZ HAVZASI

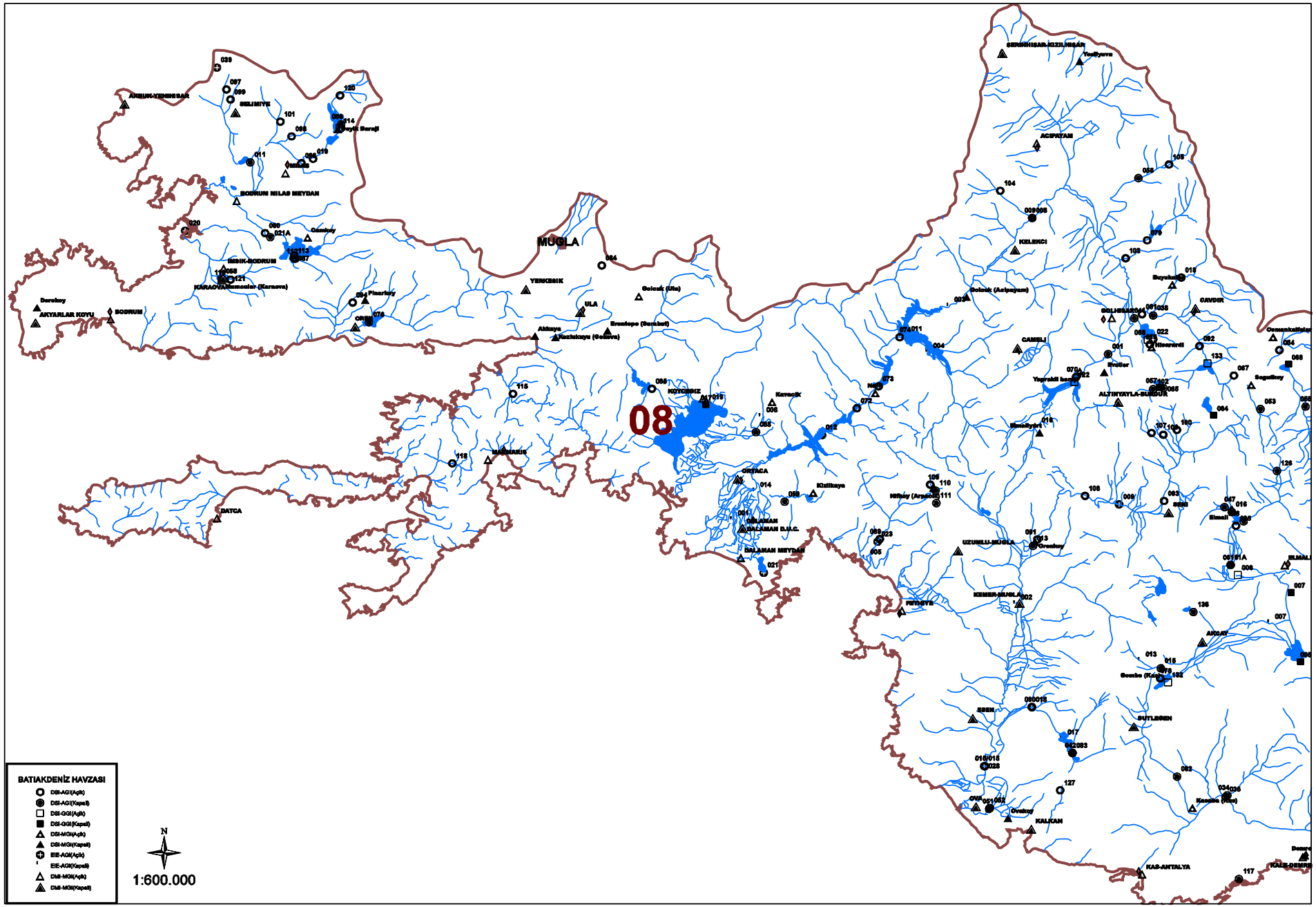
08
MUĞLA
BATIAKDENİZ HAVZASI
DSİ-AGİ(Açık)
DSİ-AGİ(Kapalı)
DSİ-GGİ(Açık)
DSİ-GGİ(Kapalı)
DSİ-MGİ(Açık)
DSİ-MGİ(Kapalı)
EİE-AGİ(Açık)
EİE-AGİ(Kapalı)
DMİ-MGİ(Açık)
DMİ-MGİ(Kapalı)
N
1:600.000

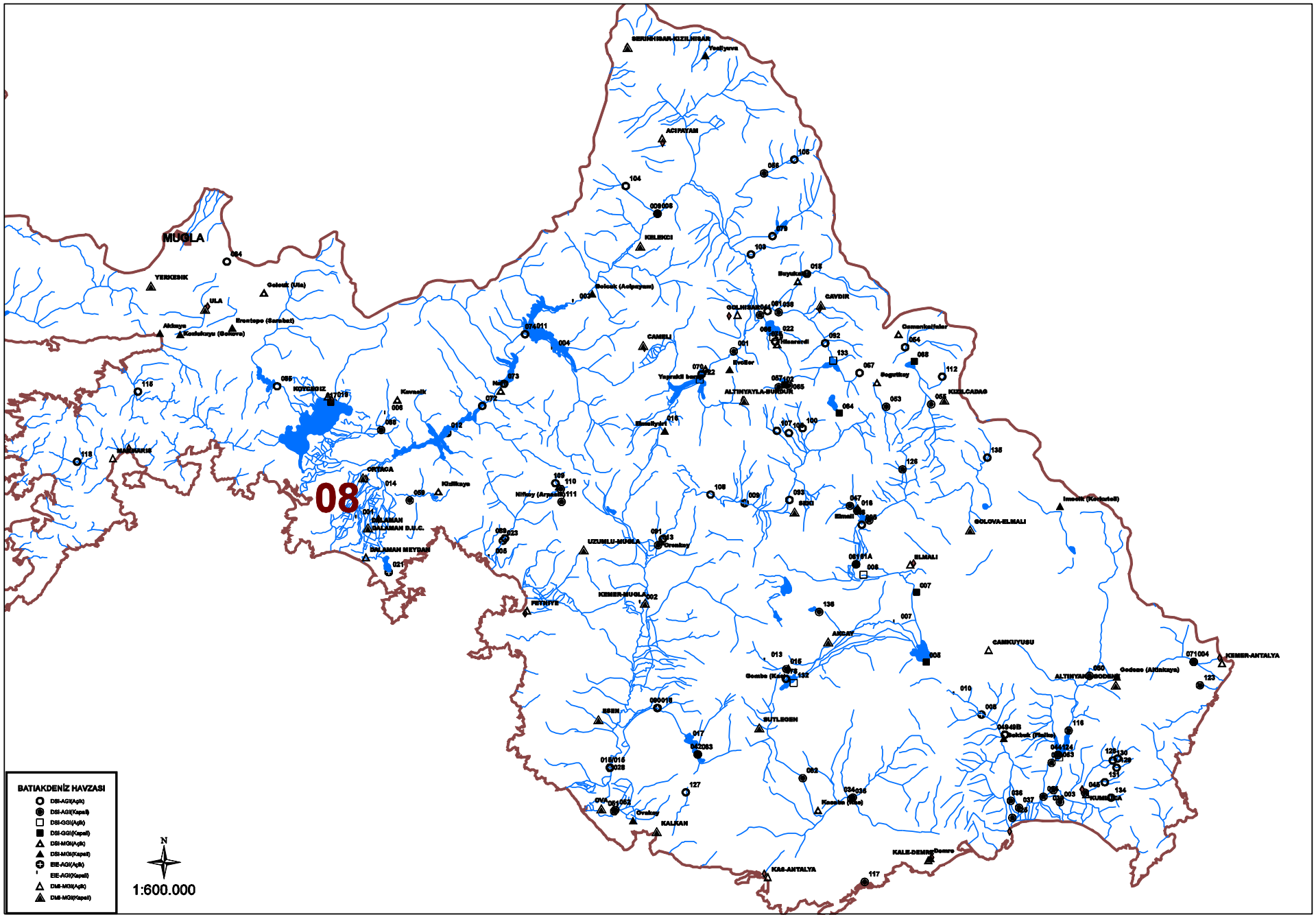
08
MUĞLA
BATIAKDENİZ HAVZASI
DSİ-AGİ(Açık)
DSİ-AGİ(Kapalı)
DSİ-GGİ(Açık)
DSİ-GGİ(Kapalı)
DSİ-MGİ(Açık)
DSİ-MGİ(Kapalı)
EİE-AGİ(Açık)
EİE-AGİ(Kapalı)
DMİ-MGİ(Açık)
DMİ-MGİ(Kapalı)
N
1:600.000

08. Bati Akdeniz Havzasi

D08A009 KİRENİŞ ÇAYI. ÇAKIR KÖPRÜSÜ

YERİ : **ACIPAYAM - KELEKÇİ YOLUNUN 16.KM SİNDEKİ ÇAKIR KÖPRÜSÜNDEDİR.**
29°20'0" Doğu - 37°19'0" Kuzey

YAĞIŞ ALANI : **2715,00 km2** **YAKLAŞIK KOT : 815 m**

GÖZLEM SÜRESİ : **01.02.1969 - 30.09.2006**

ORTALAMA AKIMLAR : **Gözlem süresinde 8.716 m3/sn. (32 Yıllık) 2006 Su yılında 3.582 m3/sn.**

ANLIK EN ÇOK VE EN AZ AKIMLAR:

2006 Su yılında anlık ençok akım	**:**	**16.4**	**m3/sn**	**14.03.2006**
2006 Su yılında anlık enaz akım	**:**	**0.260**	**m3/sn**	**06.08.2006**
Gözlem süresinde anlık ençok akım	**:**	**180.**	**m3/sn**	**22.11.1969**
Gözlem süresinde anlık enaz akım	**:**	**0.150**	**m3/sn**	**24.07.2001**

Akımlar 01 Ekim 2005 'den 30 Eylül 2006' a kadar m3/sn olarak

Gün	Ekim	Kasım	Aralık	Ocak	Şubat	Mart	Nisan	Mayıs	Haziran	Temmuz	Ağustos	Eylül
01	2.80	4.68	4.68	4.68	4.96	5.80	7.06	3.56	1.19	2.80	0.336	0.876
02	3.14	3.98	4.68	4.68	4.96	5.80	6.78	2.90	1.19	2.40	0.317	0.982
03	5.10	3.98	4.68	4.54	4.96	5.80	6.50	2.40	1.19	2.40	0.317	0.982
04	3.84	4.40	4.54	3.98	4.82	6.08	6.36	2.40	1.04	2.40	0.279	0.823
05	3.14	4.40	4.68	4.40	4.82	5.80	6.36	3.56	1.04	2.50	0.279	0.876
06	3.28	4.26	4.54	4.68	4.96	5.66	6.22	3.28	1.04	2.50	0.279	0.929
07	3.00	4.26	4.54	5.10	5.94	5.66	5.94	2.70	1.04	2.50	0.431	0.876
08	2.80	4.68	4.54	4.96	6.22	6.22	5.80	2.50	1.09	2.30	0.738	0.770
09	2.50	4.54	4.54	4.68	6.08	6.92	5.52	2.50	1.25	2.30	0.770	0.770
10	2.60	4.26	4.54	4.68	5.80	6.50	5.38	2.50	1.30	2.30	0.876	0.823
11	2.70	4.26	4.54	4.54	6.08	6.08	5.24	2.40	1.44	2.20	0.876	0.876
12	3.00	4.26	4.54	4.54	6.36	6.08	5.10	2.40	1.37	2.10	0.823	0.823
13	3.42	4.26	4.40	4.54	6.22	6.92	4.82	2.40	1.44	2.00	0.876	0.823
14	2.80	4.26	4.54	4.54	5.94	11.8	4.40	2.30	1.79	1.93	0.823	0.823
15	2.70	4.26	4.68	4.40	5.66	15.1	5.66	2.20	1.93	1.86	0.823	0.876
16	2.60	3.42	4.68	4.40	5.52	11.8	6.08	1.93	1.86	1.79	0.823	0.823
17	2.70	3.00	4.54	3.98	5.52	10.6	5.80	1.79	1.72	1.72	0.770	0.982
18	2.90	6.08	4.68	4.12	5.52	9.80	4.68	1.58	1.72	1.65	0.823	1.51
19	2.90	8.64	5.94	4.26	5.52	9.20	4.54	1.58	2.10	1.25	0.823	1.44
20	2.80	8.28	6.36	4.68	5.38	8.64	3.84	1.65	1.93	0.876	0.770	1.09
21	2.80	6.92	5.52	4.54	5.38	8.28	2.80	1.51	1.72	0.823	0.770	0.823
22	2.70	5.94	5.10	4.54	5.38	8.46	2.70	1.44	1.37	0.823	0.770	0.929
23	2.40	5.52	4.96	4.68	5.38	8.28	2.50	1.37	1.37	0.823	0.738	1.25
24	2.20	5.38	4.82	5.24	5.38	8.82	4.82	1.30	1.30	0.823	0.706	1.79
25	2.00	5.24	4.68	5.80	5.38	9.20	4.26	1.25	1.65	0.823	0.706	2.20
26	2.10	5.10	4.68	6.22	5.38	9.20	4.68	1.25	2.90	0.823	0.706	2.00
27	2.00	4.54	4.68	5.52	5.80	8.46	4.40	1.51	4.26	0.823	0.738	1.79
28	2.00	4.68	4.68	5.24	5.80	8.10	3.84	1.44	5.38	0.770	0.770	2.10
29	2.00	4.68	4.68	5.10	-----	7.74	3.56	1.30	5.10	0.546	0.929	2.00
30	2.20	4.54	4.68	4.96	-----	7.56	3.56	1.25	3.42	0.336	0.876	2.10
31	3.00	-----	4.68	4.96	-----	7.38	-----	1.19	-----	0.336	0.876	-----
Maks.	5.38	10.4	7.38	6.36	6.50	16.4	8.64	4.12	6.78	3.28	2.00	2.30
Min.	2.00	3.00	4.40	3.70	4.82	5.52	1.65	1.19	0.982	0.317	0.260	0.770
Ortalama	2.78	4.89	4.77	4.75	5.54	7.99	4.97	2.04	1.90	1.60	0.692	1.19
LT/SN/Km2	1.02	1.80	1.76	1.75	2.04	2.94	1.83	0.753	0.702	0.588	0.255	0.439
AKIM mm.	2.74	4.67	4.71	4.68	4.94	7.88	4.75	2.02	1.82	1.58	0.682	1.14
MİL. M3	7.44	12.7	12.8	12.7	13.4	21.4	12.9	5.47	4.94	4.28	1.85	3.09

SU YILI (2006) YILLIK TOPLAM AKIM 112.97 MİLYON M3 42 MM. 1.3 LT/SN/Km2

08. Bati Akdeniz Havzasi

D08A018 BALLIK D. BALLIK BOĞAZI

YERİ : TEFENNİ İLÇESİNİN ÇAVDIR BUCAĞINA 10 KM MESAFEDEKİ BÜYÜK ALANLI KÖYÜNÜN 2900 M MENBASINDADIR
HARİTA PAFTA NO: N23-D2
29°40'0" Doğu - 37°13'0" Kuzey

YAĞIŞ ALANI : 126,20 km2 YAKLAŞIK KOT : 1091 m

GÖZLEM SÜRESİ : 01.10.1961 - 30.09.2006

ORTALAMA AKIMLAR : Gözlem süresinde 0.615 m3/sn. (9 Yıllık) 2006 Su yılında 0.489 m3/sn.

ANLIK EN ÇOK VE EN AZ AKIMLAR:

2006 Su yılında anlık ençok akım	:	1.01	m3/sn	09.10.2005
2006 Su yılında anlık enaz akım	:	0.270	m3/sn	11.07.2006
Gözlem süresinde anlık ençok akım	:	62.0	m3/sn	29.12.1964
Gözlem süresinde anlık enaz akım	:	0.072	m3/sn	28.12.2002

4. Anahtar Eğrisi (Seviyeler cm olarak)

Seviye	Akım	Seviye	Akım	Seviye	Akım	Seviye	Akım
20	0.094	40	0.780	90	6.5	140	17.5
21	0.108	50	1.4	100	8.4	180	35.0
25	0.185	60	2.5	110	10.3		
30	0.320	70	3.7	120	12.5		
35	0.520	80	5.0	130	15.0		

Akımlar 01 Ekim 2005 'den 30 Eylül 2006' a kadar m3/sn olarak

Gün	Ekim	Kasım	Aralık	Ocak	Şubat	Mart	Nisan	Mayıs	Haziran	Temmuz	Ağustos	Eylül
01	0.370	0.430	0.580	0.580	0.620	0.620	0.700	0.700	0.320	0.320	0.270	0.320
02	0.370	0.430	0.580	0.580	0.620	0.620	0.660	0.660	0.320	0.320	0.270	0.300
03	0.370	0.430	0.580	0.620	0.620	0.620	0.620	0.660	0.320	0.320	0.270	0.300
04	0.370	0.460	0.580	0.620	0.620	0.700	0.620	0.700	0.320	0.320	0.270	0.320
05	0.370	0.430	0.580	0.620	0.620	0.700	0.620	0.740	0.320	0.320	0.270	0.320
06	0.370	0.460	0.580	0.620	0.620	0.700	0.620	0.795	0.320	0.300	0.270	0.320
07	0.370	0.460	0.580	0.620	0.620	0.700	0.580	0.795	0.320	0.300	0.270	0.320
08	0.370	0.460	0.580	0.620	0.620	0.700	0.580	0.740	0.320	0.300	0.270	0.320
09	1.01	0.460	0.580	0.620	0.620	0.740	0.580	0.660	0.320	0.300	0.270	0.320
10	0.950	0.460	0.580	0.620	0.620	0.740	0.580	0.660	0.320	0.300	0.270	0.320
11	0.370	0.460	0.580	0.620	0.620	0.700	0.580	0.660	0.320	0.270	0.270	0.320
12	0.370	0.500	0.580	0.620	0.620	0.700	0.580	0.660	0.320	0.270	0.270	0.320
13	0.370	0.500	0.580	0.620	0.620	0.700	0.580	0.660	0.320	0.270	0.270	0.320
14	0.430	0.500	0.580	0.620	0.620	0.950	0.580	0.620	0.320	0.270	0.270	0.320
15	0.500	0.535	0.580	0.620	0.620	0.950	0.580	0.580	0.320	0.270	0.270	0.320
16	0.500	0.535	0.580	0.620	0.620	0.900	0.620	0.535	0.320	0.270	0.270	0.320
17	0.500	0.535	0.580	0.620	0.620	0.740	0.700	0.535	0.320	0.270	0.270	0.320
18	0.500	0.535	0.580	0.620	0.620	0.700	0.700	0.400	0.320	0.270	0.270	0.320
19	0.500	0.660	0.580	0.620	0.620	0.700	0.660	0.400	0.320	0.270	0.270	0.320
20	0.500	0.580	0.580	0.620	0.620	0.700	0.660	0.370	0.320	0.270	0.270	0.320
21	0.500	0.620	0.580	0.620	0.620	0.700	0.660	0.370	0.320	0.270	0.270	0.320
22	0.500	0.580	0.580	0.620	0.620	0.700	0.620	0.370	0.320	0.270	0.270	0.320
23	0.500	0.535	0.580	0.620	0.620	0.660	0.620	0.370	0.320	0.270	0.270	0.320
24	0.500	0.535	0.580	0.620	0.620	0.660	0.700	0.370	0.320	0.270	0.270	0.320
25	0.500	0.535	0.580	0.620	0.620	0.700	0.700	0.370	0.320	0.270	0.270	0.320
26	0.460	0.535	0.580	0.620	0.620	0.660	0.700	0.370	0.320	0.270	0.270	0.320
27	0.430	0.535	0.580	0.620	0.620	0.660	0.700	0.370	0.320	0.270	0.270	0.320
28	0.430	0.535	0.580	0.620	0.620	0.660	0.700	0.370	0.320	0.270	0.270	0.320
29	0.430	0.535	0.580	0.620	-----	0.660	0.700	0.370	0.320	0.270	0.270	0.320
30	0.430	0.535	0.580	0.620	-----	0.660	0.700	0.370	0.320	0.270	0.270	0.320
31	0.430	-----	0.580	0.620	-----	0.700	-----	0.320	-----	0.270	0.270	-----
Maks.	1.01	0.660	0.580	0.620	0.620	0.950	0.700	0.795	0.320	0.370	0.270	0.320
Min.	0.370	0.430	0.500	0.500	0.535	0.535	0.580	0.320	0.320	0.270	0.270	0.300
Ortalama	0.470	0.510	0.580	0.617	0.620	0.710	0.640	0.534	0.320	0.283	0.270	0.319
LT/SN/Km2	3.72	4.04	4.60	4.89	4.91	5.62	5.07	4.23	2.54	2.24	2.14	2.53
AKIM mm.	9.98	10.5	12.3	13.1	11.9	15.1	13.1	11.3	6.57	6.00	5.73	6.55
MİL. M3	1.26	1.32	1.55	1.65	1.50	1.90	1.66	1.43	0.829	0.758	0.723	0.826

SU YILI (2006) YILLIK TOPLAM AKIM 15.41 MİLYON M3 122 MM. 3.9 LT/SN/Km2

08. Bati Akdeniz Havzasi

D08A019 SARIÇAY KOCAKAVAK

YERİ : **MUĞLA-MİLAS'A 6.KM SİNDEKİ YUSUFÇA KÖYÜNDEDİR.**
27°50'0" Doğu - 37°20'0" Kuzey

YAĞIŞ ALANI : **145,00 km2** **YAKLAŞIK KOT : 66 m**

GÖZLEM SÜRESİ : **31.07.1961 - 30.09.2006**

ORTALAMA AKIMLAR : **Gözlem süresinde 1.067 m3/sn. (32 Yıllık) 2006 Su yılında 1.067 m3/sn.**

ANLIK EN ÇOK VE EN AZ AKIMLAR:

2006 Su yılında anlık ençok akım	:	**27.9**	**m3/sn**	**14.03.2006**
2006 Su yılında anlık enaz akım	:	**0.018**	**m3/sn**	**21.09.2006**
Gözlem süresinde anlık ençok akım	:	**220.**	**m3/sn**	**17.12.1981**
Gözlem süresinde anlık enaz akım	:	**0.000**	**m3/sn**	**01.10.1983**

Akımlar 01 Ekim 2005 'den 30 Eylül 2006' a kadar m3/sn olarak

Gün	Ekim	Kasım	Aralık	Ocak	Şubat	Mart	Nisan	Mayıs	Haziran	Temmuz	Ağustos	Eylül
01	0.320	0.048	0.131	0.252	0.207	3.19	0.320	0.131	0.076	0.400	1.53	1.37
02	0.048	0.048	0.121	0.207	0.207	1.85	0.320	0.142	1.98	0.207	1.47	1.37
03	0.042	0.048	0.110	0.193	0.180	1.85	0.284	0.153	1.98	0.207	1.47	1.37
04	0.042	0.048	0.110	0.193	0.180	1.85	0.284	0.153	1.98	0.220	1.47	1.37
05	0.042	0.048	0.110	0.400	0.180	1.78	0.284	0.153	1.92	0.142	1.47	1.37
06	0.042	0.048	0.110	0.423	2.12	1.10	0.252	0.142	0.166	2.12	1.47	1.37
07	0.042	0.048	0.110	0.380	6.01	0.340	0.236	0.121	0.121	2.34	1.47	1.37
08	0.042	0.048	0.110	0.284	2.34	1.42	0.236	0.110	0.121	2.34	1.42	1.37
09	0.042	0.048	0.110	0.236	0.924	1.32	0.236	0.110	0.121	2.34	1.42	1.37
10	0.042	0.048	0.110	0.207	1.42	0.538	0.236	0.110	0.121	2.34	1.37	1.37
11	0.042	0.048	0.110	0.180	5.49	0.423	0.236	0.121	0.121	2.34	1.37	1.37
12	0.042	0.054	0.110	0.153	6.56	0.423	0.236	0.091	0.121	2.34	1.42	1.32
13	0.042	0.054	0.110	0.142	1.71	3.46	0.193	0.076	1.98	2.25	1.42	1.37
14	0.042	0.054	0.121	0.131	1.92	13.7	0.193	0.068	1.26	2.25	1.37	1.32
15	0.042	0.054	0.446	0.131	4.66	9.98	0.220	0.068	0.131	2.34	1.37	1.37
16	0.042	0.054	0.193	0.131	4.55	7.84	0.207	0.068	0.131	2.25	1.37	1.37
17	0.042	0.048	0.180	0.131	4.55	6.27	0.193	0.068	0.131	2.25	1.37	1.37
18	0.042	0.320	0.180	0.131	4.77	5.49	0.193	0.068	0.131	2.05	1.37	1.32
19	0.036	0.091	5.36	0.153	4.44	5.10	0.180	0.068	0.131	1.58	1.37	0.882
20	0.042	0.284	0.561	0.607	4.44	4.55	0.166	0.068	0.131	1.53	1.37	0.121
21	0.042	0.091	0.340	0.268	4.33	4.33	0.166	0.060	0.131	1.53	1.37	0.060
22	0.042	0.054	0.300	0.207	4.33	4.22	0.166	0.060	0.131	1.53	1.37	0.068
23	0.042	0.054	0.252	0.268	4.22	4.22	0.166	0.060	2.12	1.53	1.37	0.068
24	0.048	0.054	0.236	0.584	4.33	4.22	0.166	0.060	3.10	1.53	1.37	1.98
25	0.048	0.068	0.236	2.68	4.22	4.11	0.153	0.060	3.10	1.53	1.37	0.131
26	0.048	3.73	0.207	0.584	4.33	3.91	0.142	0.060	3.10	1.53	1.37	0.083
27	0.048	0.423	0.193	0.400	4.33	2.18	0.131	0.068	3.10	1.53	1.37	0.076
28	0.048	0.207	0.193	0.320	4.22	0.360	0.131	0.068	3.10	1.53	1.37	0.076
29	0.048	0.153	0.193	0.284	-----	0.360	0.131	0.068	2.76	1.47	1.37	0.110
30	0.048	0.142	0.193	0.252	-----	0.360	0.131	0.068	2.42	1.53	1.37	0.091
31	0.048	-----	0.193	0.220	-----	0.320	-----	0.068	-----	1.47	1.37	-----
Maks.	4.22	17.3	26.1	9.28	27.3	27.9	0.798	0.166	3.55	2.51	1.53	6.14
Min.	0.036	0.042	0.099	0.076	0.180	0.300	0.131	0.036	0.048	0.142	1.32	0.018
Ortalama	0.053	0.217	0.356	0.346	3.26	3.26	0.206	0.090	1.20	1.63	1.40	0.942
LT/SN/Km2	0.362	1.50	2.46	2.39	22.5	22.5	1.42	0.620	8.26	11.2	9.66	6.50
AKIM mm.	0.970	3.88	6.58	6.39	54.3	60.2	3.69	1.66	21.4	30.1	25.9	16.8
MİL. M3	0.141	0.563	0.954	0.927	7.88	8.73	0.535	0.241	3.10	4.37	3.75	2.44

SU YILI (2006) YILLIK TOPLAM AKIM 33.63 MİLYON M3 232 MM. 7.4 LT/SN/Km2

08. Bati Akdeniz Havzasi

D08A049 BAŞGÖZ Ç. GÖKBÜK

YERİ : **ELMALI-FİNİKE YOLUNUN 17 KM. DEN SOLA AYRILAN YOLUN 1 KM.GÖKBÜK KÖYÜ KÖPRÜSÜNDEDİR**
30°27'29" Doğu - 36°27'30" Kuzey

YAĞIŞ ALANI : **222,20 km2** **YAKLAŞIK KOT : 208 m**

GÖZLEM SÜRESİ : **25.03.1963 - 30.09.2006**

ORTALAMA AKIMLAR : **Gözlem süresinde 3.699 m3/sn. (39 Yıllık) 2006 Su yılında 1.867 m3/sn.**

ANLIK EN ÇOK VE EN AZ AKIMLAR:

2006 Su yılında anlık ençok akım	**:**	**18.7**	**m3/sn**	**14.03.2006**
2006 Su yılında anlık enaz akım	**:**	**0.973**	**m3/sn**	**06.09.2006**
Gözlem süresinde anlık ençok akım	**:**	**191.**	**m3/sn**	**22.01.2004**
Gözlem süresinde anlık enaz akım	**:**	**0.170**	**m3/sn**	**05.01.1974**

Akımlar 01 Ekim 2005 'den 30 Eylül 2006' a kadar m3/sn olarak

Gün	Ekim	Kasım	Aralık	Ocak	Şubat	Mart	Nisan	Mayıs	Haziran	Temmuz	Ağustos	Eylül
01	1.87	2.03	1.62	1.62	1.75	1.52	1.62	1.84	1.49	1.39	1.07	1.07
02	1.87	1.87	1.62	1.62	1.75	1.52	1.62	1.84	1.60	1.39	1.07	1.07
03	1.87	2.03	1.62	1.62	1.75	1.52	1.62	1.84	1.72	1.60	1.07	1.07
04	1.87	2.03	1.62	1.62	1.75	1.52	2.03	1.84	1.72	1.49	1.07	1.07
05	1.87	2.03	1.62	1.62	1.75	1.52	5.13	1.72	1.72	1.49	1.07	1.07
06	1.87	1.87	1.62	1.62	1.87	1.52	11.0	1.84	1.60	1.49	1.07	0.973
07	1.87	2.03	1.62	1.62	2.28	1.41	7.99	1.72	1.60	1.49	1.07	0.973
08	1.87	1.87	1.62	1.62	3.04	1.52	7.99	1.72	1.72	1.49	1.07	0.973
09	1.87	1.87	1.62	1.62	2.28	1.52	7.99	1.72	1.72	1.49	1.07	0.973
10	1.87	1.87	1.62	1.62	2.28	1.52	8.90	1.60	1.72	1.49	1.07	0.973
11	1.87	1.87	1.62	1.52	3.85	1.52	8.66	1.72	1.60	1.39	1.07	0.973
12	1.87	1.87	1.62	1.52	3.24	2.16	7.47	1.72	1.49	1.39	1.07	0.973
13	1.87	1.75	1.62	1.52	2.43	3.64	7.29	1.72	1.49	1.39	1.07	0.973
14	2.03	1.87	1.62	1.52	2.16	7.43	6.21	1.72	1.49	1.28	1.07	0.973
15	2.16	1.87	1.62	1.52	2.03	4.07	6.41	1.60	1.49	1.28	1.07	0.973
16	2.16	1.87	1.62	1.52	2.03	3.24	6.41	1.72	1.49	1.28	1.07	0.973
17	2.16	1.87	1.62	1.52	2.03	2.89	7.11	1.84	1.49	1.28	1.07	0.973
18	2.03	2.03	2.16	1.52	2.03	2.74	1.96	1.84	1.49	1.28	1.07	0.973
19	2.03	1.87	2.28	1.52	1.75	2.89	1.96	1.72	1.49	1.28	1.07	0.973
20	2.03	2.03	1.62	1.52	1.52	2.74	1.96	1.72	1.49	1.18	1.07	0.973
21	2.03	1.87	1.62	1.52	1.52	2.74	1.96	1.72	1.49	1.18	1.07	0.973
22	2.03	1.87	1.62	1.52	1.52	2.58	1.96	1.72	1.49	1.18	1.07	0.973
23	2.03	1.87	1.62	2.89	1.52	2.43	1.96	1.60	1.39	1.18	1.07	0.973
24	2.03	1.87	1.62	2.58	1.52	2.74	1.84	1.60	1.39	1.18	1.07	0.973
25	2.03	1.87	1.62	2.89	1.52	2.28	1.84	1.60	1.39	1.18	1.07	0.973
26	1.87	1.87	1.62	2.16	1.52	2.28	1.84	1.60	1.39	1.07	1.07	0.973
27	1.87	1.62	1.62	1.87	1.52	1.75	1.84	1.60	1.39	1.07	1.07	0.973
28	2.03	1.62	1.75	1.75	1.52	1.75	1.84	1.49	1.39	1.07	1.07	0.973
29	1.87	1.62	1.62	1.75	-----	1.75	1.84	1.49	1.39	1.07	1.07	0.973
30	2.03	1.62	1.62	1.75	-----	1.75	1.84	1.49	1.39	1.07	1.07	0.973
31	2.03	-----	1.62	1.75	-----	1.75	-----	1.49	-----	1.07	1.07	-----
Maks.	3.04	2.74	5.13	5.39	5.39	18.7	11.4	2.48	2.08	2.20	1.07	1.07
Min.	1.87	1.62	1.62	1.52	1.52	1.41	1.62	1.39	1.39	1.07	1.07	0.973
Ortalama	1.96	1.87	1.66	1.74	1.99	2.33	4.34	1.69	1.52	1.30	1.07	0.989
LT/SN/Km2	8.82	8.42	7.48	7.81	8.96	10.5	19.5	7.61	6.86	5.83	4.82	4.45
AKIM mm.	23.6	21.8	20.0	20.9	21.7	28.1	50.6	20.4	17.8	15.6	12.9	11.5
MİL. M3	5.25	4.85	4.45	4.65	4.82	6.24	11.2	4.53	3.95	3.47	2.87	2.56

SU YILI (2006) YILLIK TOPLAM AKIM 58.84 MİLYON M3 265 MM. 8.4 LT/SN/Km2

08. Bati Akdeniz Havzasi

D08A061 MÜMÜR D. MÜMÜR

YERİ : **EMALI YUVA KÖYÜ YOLUNUN 16 KM.SİNDEN SAĞA AYRILAN YOLUN 2 KMSINDEKI GEÇIT KÖPRÜSÜNÜN 2 KM. MEMBAĞINDADIR.**
29°48'0" Doğu - 36°44'0" Kuzey

YAĞIŞ ALANI : **260,17 km2** **YAKLAŞIK KOT : 1030 m**

GÖZLEM SÜRESİ : **22.11.1969 - 30.09.2006**

ORTALAMA AKIMLAR : **Gözlem süresinde 1.196 m3/sn. (36 Yıllık) 2006 Su yılında 0.500 m3/sn.**

ANLIK EN ÇOK VE EN AZ AKIMLAR:

2006 Su yılında anlık ençok akım	**:**	**17.0**	**m3/sn**	**15.04.2006**
2006 Su yılında anlık enaz akım	**:**	**0.000**	**m3/sn**	**01.10.2005**
Gözlem süresinde anlık ençok akım	**:**	**36.0**	**m3/sn**	**27.03.1980**
Gözlem süresinde anlık enaz akım	**:**	**0.000**	**m3/sn**	**10.08.1972**

Akımlar 01 Ekim 2005 'den 30 Eylül 2006' a kadar m3/sn olarak

Gün	Ekim	Kasım	Aralık	Ocak	Şubat	Mart	Nisan	Mayıs	Haziran	Temmuz	Ağustos	Eylül
01	KURU	KURU	KURU	KURU	KURU	KURU	3.50	1.40	0.014	0.240	KURU	KURU
02	KURU	KURU	KURU	KURU	KURU	KURU	3.50	1.40	0.001	0.190	KURU	KURU
03	KURU	KURU	KURU	KURU	KURU	KURU	3.50	1.40	KURU	0.100	KURU	KURU
04	KURU	KURU	KURU	KURU	KURU	KURU	3.40	1.40	KURU	0.300	KURU	KURU
05	KURU	KURU	KURU	KURU	KURU	KURU	3.30	1.30	KURU	0.360	KURU	KURU
06	KURU	KURU	KURU	KURU	KURU	KURU	3.20	1.20	KURU	0.240	KURU	KURU
07	KURU	KURU	KURU	KURU	KURU	0.001	3.30	1.05	KURU	0.190	KURU	KURU
08	KURU	KURU	KURU	KURU	0.014	0.100	3.40	0.950	KURU	0.100	KURU	KURU
09	KURU	KURU	KURU	KURU	0.100	0.140	3.30	0.950	KURU	0.070	KURU	KURU
10	KURU	KURU	KURU	KURU	0.070	0.070	3.20	0.950	KURU	0.014	KURU	KURU
11	KURU	KURU	KURU	KURU	0.044	0.026	3.30	0.870	KURU	KURU	KURU	KURU
12	KURU	KURU	KURU	KURU	0.070	0.026	3.20	0.800	KURU	KURU	KURU	KURU
13	KURU	KURU	KURU	KURU	0.044	KURU	3.30	0.710	KURU	KURU	KURU	KURU
14	KURU	KURU	KURU	KURU	0.044	0.800	3.30	0.570	KURU	KURU	KURU	KURU
15	KURU	KURU	KURU	KURU	0.026	1.05	6.40	2.60	KURU	KURU	KURU	KURU
16	KURU	KURU	KURU	KURU	0.026	0.870	5.20	6.50	KURU	KURU	KURU	KURU
17	KURU	KURU	KURU	KURU	0.026	0.870	4.80	3.90	KURU	KURU	KURU	KURU
18	KURU	KURU	KURU	KURU	0.026	1.05	4.40	0.430	KURU	KURU	KURU	KURU
19	KURU	KURU	KURU	KURU	0.026	1.20	3.90	0.360	KURU	KURU	KURU	KURU
20	KURU	KURU	KURU	KURU	0.026	1.40	3.60	0.240	KURU	KURU	KURU	KURU
21	KURU	KURU	KURU	KURU	0.026	2.10	3.40	0.300	KURU	KURU	KURU	KURU
22	KURU	KURU	KURU	KURU	0.014	2.30	3.20	0.240	KURU	KURU	KURU	KURU
23	KURU	KURU	KURU	KURU	KURU	2.90	3.50	0.190	KURU	KURU	KURU	KURU
24	KURU	KURU	KURU	KURU	KURU	3.60	3.30	0.100	KURU	KURU	KURU	KURU
25	KURU	KURU	KURU	KURU	KURU	3.50	3.00	0.070	0.001	KURU	KURU	KURU
26	KURU	KURU	KURU	0.026	KURU	3.40	2.70	0.044	0.070	KURU	KURU	KURU
27	KURU	KURU	KURU	0.014	KURU	3.60	2.30	0.044	0.300	KURU	KURU	KURU
28	KURU	KURU	KURU	KURU	KURU	3.70	2.30	0.044	1.70	KURU	KURU	KURU
29	KURU	KURU	KURU	KURU	-----	3.60	2.30	0.026	0.640	KURU	KURU	KURU
30	KURU	KURU	KURU	KURU	-----	3.70	1.90	0.026	0.300	KURU	KURU	KURU
31	KURU	-----	KURU	KURU	-----	3.90	-----	0.026	-----	KURU	KURU	-----
Maks.	KURU	KURU	KURU	0.026	0.100	4.70	17.0	7.20	3.90	0.640	KURU	KURU
Min.	KURU	KURU	KURU	KURU	KURU	KURU	1.55	0.014	KURU	KURU	KURU	KURU
Ortalama	KURU	KURU	KURU	0.001	0.021	1.42	3.43	0.971	0.101	0.058	KURU	KURU
LT/SN/Km2	0.000	0.000	0.000	0.005	0.080	5.44	13.2	3.73	0.388	0.224	0.000	0.000
AKIM mm.	0.000	0.000	0.000	0.013	0.193	14.6	34.2	9.99	1.00	0.599	0.000	0.000
MİL. M3	0.000	0.000	0.000	0.003	0.050	3.79	8.89	2.60	0.261	0.156	0.000	0.000

SU YILI (2006) YILLIK TOPLAM AKIM 15.75 MİLYON M3 61 MM. 1.9 LT/SN/Km2

08. Bati Akdeniz Havzasi

D08A067 SÖGÜT G. ÇIKIŞ

YERİ : BURDUR ÇAVDIR-SÖĞÜT YOLUNUN 19.6 KM SİNDEKİ GÖL TAHLİYE TÜNELİNİN 500 M. MANSABINDADIR
HARİTA PAFTA NO: N23-C4
29°47'15" Doğu - 37°3'20" Kuzey

YAĞIŞ ALANI : 444,90 km2 YAKLAŞIK KOT : 1396 m

GÖZLEM SÜRESİ : 01.03.1970 - 30.09.2006

ORTALAMA AKIMLAR : Gözlem süresinde 0.881 m3/sn. (30 Yıllık) 2006 Su yılında 0.268 m3/sn.

ANLIK EN ÇOK VE EN AZ AKIMLAR:

2006 Su yılında anlık ençok akım	:	1.25	m3/sn	17.04.2006
2006 Su yılında anlık enaz akım	:	0.034	m3/sn	25.09.2006
Gözlem süresinde anlık ençok akım	:	16.0	m3/sn	21.03.1981
Gözlem süresinde anlık enaz akım	:	0.000	m3/sn	01.10.1971

9. Anahtar Eğrisi (Seviyeler cm olarak)

Seviye	Akım	Seviye	Akım	Seviye	Akım	Seviye	Akım
13	0.001	37	0.230	54	0.850	90	3.2
25	0.039	39	0.280	58	1.0	110	5.1
31	0.110	42	0.370	62	1.2	130	7.1
33	0.145	46	0.510	66	1.4	140	8.2
35	0.180	50	0.670	70	1.7	150	9.3

Akımlar 01 Ekim 2005 'den 30 Eylül 2006' a kadar m3/sn olarak

Gün	Ekim	Kasım	Aralık	Ocak	Şubat	Mart	Nisan	Mayıs	Haziran	Temmuz	Ağustos	Eylül
01	0.180	0.110	0.280	0.305	0.280	0.370	0.550	0.750	0.050	0.050	0.061	0.039
02	0.125	0.110	0.280	0.305	0.280	0.370	0.510	0.670	0.050	0.050	0.061	0.039
03	0.125	0.110	0.280	0.305	0.280	0.370	0.510	0.670	0.160	0.050	0.061	0.039
04	0.110	0.110	0.280	0.305	0.280	0.370	0.475	0.670	0.110	0.050	0.061	0.039
05	0.110	0.125	0.280	0.305	0.280	0.370	0.440	0.670	0.061	0.050	0.061	0.039
06	0.110	0.145	0.338	0.305	0.280	0.405	0.440	0.670	0.110	0.050	0.061	0.050
07	0.110	0.160	0.510	0.305	0.370	0.405	0.440	0.670	0.180	0.050	0.061	0.050
08	0.110	0.160	0.440	0.305	0.370	0.405	0.440	0.630	0.160	0.050	0.061	0.039
09	0.110	0.145	0.440	0.305	0.370	0.405	0.405	0.590	0.160	0.050	0.061	0.039
10	0.110	0.145	0.405	0.305	0.370	0.405	0.405	0.590	0.160	0.050	0.061	0.039
11	0.110	0.145	0.370	0.305	0.370	0.405	0.405	0.590	0.160	0.050	0.061	0.039
12	0.110	0.145	0.370	0.305	0.370	0.405	0.405	0.510	0.160	0.050	0.061	0.039
13	0.110	0.145	0.338	0.305	0.370	0.405	0.370	0.510	0.338	0.050	0.061	0.039
14	0.110	0.145	0.338	0.305	0.370	0.510	0.370	0.510	0.180	0.050	0.061	0.039
15	0.110	0.145	0.338	0.305	0.370	0.670	0.370	0.510	0.050	0.050	0.061	0.039
16	0.110	0.145	0.338	0.305	0.370	0.710	0.440	0.440	0.050	0.050	0.061	0.039
17	0.110	0.145	0.338	0.305	0.370	0.710	1.25	0.440	0.050	0.050	0.050	0.039
18	0.110	0.145	0.338	0.305	0.370	0.670	1.13	0.475	0.050	0.050	0.050	0.039
19	0.110	0.180	0.338	0.305	0.370	0.630	0.940	0.440	0.050	0.050	0.050	0.039
20	0.110	0.180	0.338	0.305	0.370	0.630	0.850	0.440	0.050	0.050	0.050	0.039
21	0.110	0.180	0.370	0.338	0.370	0.630	0.750	0.440	0.050	0.050	0.050	0.072
22	0.110	0.180	0.370	0.370	0.370	0.630	0.710	0.440	0.050	0.050	0.050	0.083
23	0.110	0.200	0.405	0.338	0.370	0.590	0.670	0.405	0.050	0.050	0.083	0.083
24	0.110	0.200	0.405	0.338	0.370	0.590	0.750	0.405	0.050	0.125	0.145	0.061
25	0.110	0.200	0.405	0.338	0.370	0.590	0.985	0.405	0.050	0.061	0.180	0.034
26	0.110	0.255	0.370	0.305	0.370	0.590	0.850	0.405	0.050	0.061	0.094	0.094
27	0.110	0.255	0.338	0.305	0.370	0.590	0.800	0.370	0.050	0.061	0.094	0.083
28	0.110	0.255	0.338	0.305	0.370	0.630	0.750	0.370	0.050	0.061	0.083	0.050
29	0.110	0.255	0.338	0.305	-----	0.630	0.710	0.370	0.050	0.061	0.072	0.050
30	0.110	0.255	0.305	0.338	-----	0.630	0.670	0.370	0.050	0.061	0.039	0.039
31	0.110	-----	0.305	0.305	-----	0.590	-----	0.125	-----	0.061	0.039	-----
Maks.	0.180	0.255	0.510	0.370	0.370	0.710	1.25	0.750	0.338	0.125	0.180	0.094
Min.	0.110	0.110	0.280	0.305	0.280	0.370	0.370	0.110	0.050	0.050	0.039	0.034
Ortalama	0.113	0.169	0.352	0.312	0.351	0.526	0.626	0.502	0.095	0.055	0.068	0.048
LT/SN/Km2	0.254	0.380	0.792	0.702	0.788	1.18	1.41	1.13	0.213	0.123	0.153	0.109
AKIM mm.	0.682	0.986	2.12	1.88	1.91	3.17	3.65	3.02	0.551	0.331	0.409	0.282
MİL. M3	0.303	0.438	0.944	0.837	0.848	1.41	1.62	1.34	0.245	0.147	0.182	0.125

SU YILI (2006) YILLIK TOPLAM AKIM 8.44 MİLYON M3 19 MM. 0.6 LT/SN/Km2

08. Bati Akdeniz Havzasi

D08A070 HORZUM Ç. YAPRAKLI

YERİ : **GÖLHİSAR-İBECİK YOLUNUN 17 KM SİNDEKİ ORMAN PINARININ KARŞISINDADIR. HARİTA PAFTA NO: N23-D4**
29°27'30" Doğu - 37°2'23" Kuzey

YAĞIŞ ALANI : **459,20 km2** **YAKLAŞIK KOT : 988 m**

GÖZLEM SÜRESİ : **27.01.1973 - 30.09.2006**

ORTALAMA AKIMLAR : **Gözlem süresinde 3.848 m3/sn. (32 Yıllık) 2006 Su yılında 2.148 m3/sn.**

ANLIK EN ÇOK VE EN AZ AKIMLAR:

2006 Su yılında anlık ençok akım	:	**9.00**	**m3/sn**	**23.05.2006**
2006 Su yılında anlık enaz akım	:	**0.060**	**m3/sn**	**26.12.2005**
Gözlem süresinde anlık ençok akım	:	**190.**	**m3/sn**	**16.12.1981**
Gözlem süresinde anlık enaz akım	:	**0.000**	**m3/sn**	**19.09.1977**

4. Anahtar Eğrisi (Seviyeler cm olarak)

Seviye	Akım	Seviye	Akım	Seviye	Akım	Seviye	Akım
7	0.020	27	0.980	56	4.5	96	15.4
11	0.100	32	1.4	64	6.0	120	25.0
15	0.240	36	1.8	72	8.0	160	46.0
19	0.420	40	2.2	80	10.0	200	70.0
23	0.680	48	3.2	88	12.5		

Akımlar 01 Ekim 2005 'den 30 Eylül 2006' a kadar m3/sn olarak

Gün	Ekim	Kasım	Aralık	Ocak	Şubat	Mart	Nisan	Mayıs	Haziran	Temmuz	Ağustos	Eylül
01	0.740	0.250	0.080	0.060	0.080	0.150	0.180	0.430	8.75	2.60	5.10	5.85
02	0.740	0.250	0.080	0.060	0.080	0.150	0.180	0.295	8.75	2.20	4.70	4.03
03	0.540	0.250	0.100	0.060	0.080	0.150	0.215	0.215	8.75	2.33	4.70	3.85
04	0.480	0.250	0.100	0.080	0.100	0.150	0.215	0.215	8.75	2.33	4.70	3.70
05	0.480	0.250	0.100	0.080	0.100	0.150	0.250	0.215	8.75	2.33	4.70	3.70
06	0.480	0.250	0.125	0.080	0.150	0.150	0.250	0.215	8.75	3.00	4.50	3.70
07	0.480	0.250	0.125	0.080	0.150	0.150	0.295	0.215	8.00	2.60	4.50	3.70
08	0.480	0.250	0.125	0.080	0.150	0.150	0.295	0.215	5.85	2.00	4.50	3.70
09	0.810	0.250	0.125	0.080	0.150	0.150	0.295	0.215	5.30	2.10	4.90	3.70
10	3.13	0.250	0.125	0.080	0.150	0.150	0.295	0.215	5.30	2.20	5.50	3.70
11	3.13	0.215	0.125	0.080	0.150	0.150	0.295	0.215	5.30	3.40	5.70	3.70
12	3.13	0.215	0.125	0.080	0.150	0.150	0.295	0.215	5.30	4.50	5.70	5.85
13	3.13	0.215	0.125	0.080	0.150	0.150	0.335	0.215	5.30	6.50	5.70	5.10
14	3.13	0.180	0.100	0.080	0.150	0.150	0.295	0.180	5.30	6.25	5.70	4.70
15	3.13	0.180	0.100	0.080	0.150	0.150	0.295	0.810	5.10	6.00	5.70	4.70
16	3.13	0.180	0.100	0.080	0.150	0.150	0.385	4.03	4.70	5.70	5.50	4.70
17	3.13	0.180	0.100	0.080	0.150	0.150	0.385	4.90	4.70	5.70	5.50	4.90
18	3.13	0.180	0.100	0.080	0.150	0.150	0.385	6.25	4.70	5.70	5.50	4.90
19	2.60	0.180	0.100	0.080	0.150	0.180	0.385	7.25	4.70	5.70	6.00	4.70
20	0.480	0.180	0.080	0.080	0.150	0.180	0.430	7.50	4.70	4.70	6.50	4.70
21	0.480	0.180	0.080	0.080	0.150	0.180	0.430	8.00	4.70	4.70	6.00	4.03
22	0.480	0.180	0.080	0.080	0.150	0.180	0.540	8.75	5.10	4.50	6.00	1.80
23	0.480	0.180	0.080	0.080	0.150	0.180	0.740	9.00	5.10	4.70	6.25	0.540
24	0.480	0.180	0.080	0.080	0.150	0.180	0.870	9.00	5.10	4.70	6.25	0.540
25	0.480	0.150	0.080	0.080	0.150	0.180	0.960	9.00	5.30	4.50	6.25	0.540
26	0.430	0.150	0.060	0.080	0.150	0.180	0.960	9.00	5.30	5.10	6.00	0.540
27	0.385	0.150	0.060	0.080	0.150	0.180	0.960	9.00	5.30	5.50	6.00	0.540
28	0.335	0.125	0.060	0.080	0.150	0.180	0.960	9.00	5.10	5.50	6.00	0.540
29	0.295	0.100	0.060	0.080	-----	0.180	0.960	8.75	4.03	5.50	6.00	0.540
30	0.295	0.080	0.060	0.080	-----	0.180	0.540	8.75	3.00	5.50	6.00	0.540
31	0.295	-----	0.060	0.080	-----	0.180	-----	8.75	-----	5.50	5.85	-----
Maks.	3.13	0.250	0.125	0.080	0.150	0.180	0.960	9.00	8.75	6.50	6.50	5.85
Min.	0.295	0.080	0.060	0.060	0.080	0.150	0.180	0.180	3.00	2.00	4.50	0.540
Ortalama	1.32	0.196	0.094	0.078	0.139	0.163	0.463	4.23	5.83	4.31	5.55	3.26
LT/SN/Km2	2.87	0.427	0.204	0.170	0.303	0.354	1.01	9.20	12.7	9.38	12.1	7.09
AKIM mm.	7.70	1.11	0.546	0.455	0.732	0.948	2.61	24.6	32.9	25.1	32.3	18.4
MİL. M3	3.54	0.508	0.251	0.209	0.336	0.435	1.20	11.3	15.1	11.5	14.9	8.44

SU YILI (2006) YILLIK TOPLAM AKIM 67.72 MİLYON M3 147 MM. 4.7 LT/SN/Km2

08. Bati Akdeniz Havzasi

D08A073 DALAMAN Ç. NARLI

YERİ : **MUĞLA-KÖYCEĞİZ-AŞAĞI NARLI KÖYÜNDEN YUKARI NARLI YOLUNA SAPILDIĞINDA ESKİ MADEN YOLUNDAN 20 M MESAFEDEKİ ASMA KÖPRÜDEDİR.**
37°0'0" Doğu - 29°2'0" Kuzey

YAĞIŞ ALANI : **4184,00 km2** **YAKLAŞIK KOT : 300 m**

GÖZLEM SÜRESİ : **19.09.1976 - 30.09.2006**

ORTALAMA AKIMLAR : **Gözlem süresinde 26.885 m3/sn. (19 Yıllık) 2006 Su yılında 22.950 m3/sn.**

ANLIK EN ÇOK VE EN AZ AKIMLAR:

2006 Su yılında anlık ençok akım	:	**143.**	**m3/sn**	**19.12.2005**
2006 Su yılında anlık enaz akım	:	**9.80**	**m3/sn**	**27.08.2006**
Gözlem süresinde anlık ençok akım	:	**1200**	**m3/sn**	**13.12.1979**
Gözlem süresinde anlık enaz akım	:	**6.98**	**m3/sn**	**23.08.1991**

Akımlar 01 Ekim 2005 'den 30 Eylül 2006' a kadar m3/sn olarak

Gün	Ekim	Kasım	Aralık	Ocak	Şubat	Mart	Nisan	Mayıs	Haziran	Temmuz	Ağustos	Eylül
01	12.8	12.4	18.7	21.6	24.1	40.2	42.8	25.6	13.1	19.2	10.7	9.80
02	12.8	12.4	17.5	20.8	23.7	37.6	41.9	25.2	13.1	18.8	10.4	10.1
03	21.2	14.3	16.7	20.4	23.3	36.8	41.1	24.8	13.1	18.0	10.4	10.4
04	22.0	16.7	16.3	20.4	26.2	36.4	40.2	24.4	13.1	18.0	10.4	10.4
05	18.3	15.9	16.3	20.4	30.0	35.5	39.4	24.4	13.1	17.2	10.4	10.4
06	17.1	15.5	15.9	20.8	32.5	34.6	39.8	25.6	13.1	16.8	10.4	10.7
07	15.9	15.5	15.9	26.2	66.2	33.8	37.6	25.2	12.8	16.8	10.4	10.7
08	15.5	15.5	15.5	25.0	86.6	35.9	36.8	24.4	12.8	16.4	10.4	10.7
09	15.5	15.5	15.5	23.3	87.2	40.7	35.9	24.0	12.8	16.0	10.4	11.0
10	15.1	15.5	15.5	22.0	75.0	38.9	35.9	23.6	12.8	15.2	10.4	11.0
11	15.1	15.5	15.1	21.2	63.3	38.5	35.5	22.8	12.8	13.7	10.4	11.0
12	14.7	15.1	15.1	20.8	56.4	43.2	35.1	22.8	13.7	13.1	10.1	11.0
13	14.7	15.1	15.1	20.8	51.4	58.2	35.1	22.4	13.7	12.8	10.1	11.3
14	14.3	15.1	15.5	20.4	45.8	119.	35.5	22.0	13.7	12.5	10.1	11.3
15	14.3	15.5	17.5	20.0	42.8	74.0	37.7	21.2	13.4	11.9	10.1	11.3
16	14.3	15.5	17.5	20.0	39.8	62.9	38.1	21.2	13.4	11.6	10.1	11.6
17	13.9	15.9	17.1	19.6	37.6	55.9	35.0	20.8	13.1	11.3	10.1	11.6
18	13.9	24.5	52.3	19.6	37.6	51.9	33.6	20.4	13.1	11.3	10.1	11.6
19	13.9	32.1	105.	19.1	35.1	51.4	32.3	20.4	13.1	11.3	10.4	11.9
20	13.5	33.8	45.4	19.6	33.8	51.0	30.5	19.6	12.8	11.0	10.4	11.9
21	13.5	33.4	33.4	22.4	32.9	49.3	29.6	18.8	12.8	11.0	10.4	11.6
22	13.5	32.5	28.7	20.8	32.5	48.4	29.2	18.4	12.8	11.0	10.1	11.6
23	13.1	30.4	26.2	24.5	32.1	48.0	29.2	18.0	12.8	11.0	10.1	11.9
24	13.1	28.3	25.0	32.5	32.1	47.5	30.5	14.8	12.5	11.0	10.1	13.4
25	13.1	26.2	24.1	48.0	31.3	47.1	29.2	13.4	12.5	10.7	10.1	15.2
26	12.8	24.1	23.7	37.2	31.3	47.1	28.0	13.1	13.4	10.7	10.1	14.8
27	12.8	22.9	23.7	31.7	38.1	46.2	27.6	13.7	14.4	10.7	9.80	14.4
28	12.8	21.6	23.3	28.3	38.5	44.1	26.4	13.7	19.6	10.7	9.80	14.0
29	12.8	20.4	25.4	26.6	-----	43.7	26.0	13.4	20.0	10.7	9.80	14.8
30	12.4	19.6	24.5	25.8	-----	43.7	25.6	13.4	19.6	10.7	9.80	14.4
31	12.4	-----	23.3	23.7	-----	43.2	-----	13.4	-----	10.7	9.80	-----
Maks.	31.7	34.2	143.	53.7	89.4	132.	42.8	25.6	20.4	19.2	10.7	20.0
Min.	12.4	12.4	15.1	19.1	22.9	33.4	25.6	13.1	12.5	10.7	9.80	9.80
Ortalama	14.6	20.2	24.5	24.0	42.4	47.9	34.0	20.2	13.8	13.3	10.2	11.9
LT/SN/Km2	3.48	4.83	5.86	5.73	10.1	11.4	8.13	4.82	3.29	3.17	2.44	2.83
AKIM mm.	9.32	12.5	15.7	15.4	24.5	30.7	21.1	12.9	8.53	8.50	6.53	7.35
MİL. M3	39.0	52.4	65.7	64.2	103.	128.	88.2	54.0	35.7	35.6	27.3	30.7

SU YILI (2006) YILLIK TOPLAM AKIM 723.80 MİLYON M3 173 MM. 5.5 LT/SN/Km2

08. Bati Akdeniz Havzasi

D08A078 AKÇAY GÖMBE

YERİ : **GÖMBE KÖYÜNDEN 2 KM. BATIYA GİDİLEREK ISTASYONA VARILIR. GÖMBE KÖPRÜSÜNÜN 500 M MENBAĞINDADIR.**
29°39'59" Doğu - 36°32'5" Kuzey

YAĞIŞ ALANI : **45,16 km2** **YAKLAŞIK KOT : 1254 m**

GÖZLEM SÜRESİ : **01.10.1977 - 30.09.2006**

ORTALAMA AKIMLAR : **Gözlem süresinde 2.128 m3/sn. (11 Yıllık) 2006 Su yılında 0.911 m3/sn.**

ANLIK EN ÇOK VE EN AZ AKIMLAR:

2006 Su yılında anlık ençok akım	:	**7.10**	**m3/sn**	**21.01.2006**
2006 Su yılında anlık enaz akım	:	**0.050**	**m3/sn**	**26.08.2006**
Gözlem süresinde anlık ençok akım	:	**17.0**	**m3/sn**	**15.10.1977**
Gözlem süresinde anlık enaz akım	:	**0.050**	**m3/sn**	**26.08.2006**

Akımlar 01 Ekim 2005 'den 30 Eylül 2006' a kadar m3/sn olarak

Gün	Ekim	Kasım	Aralık	Ocak	Şubat	Mart	Nisan	Mayıs	Haziran	Temmuz	Ağustos	Eylül
01	0.240	0.340	0.520	0.750	0.410	0.340	1.05	2.58	2.15	0.750	0.160	0.160
02	0.520	0.340	0.520	0.750	0.410	0.160	1.05	2.58	2.15	0.750	0.160	0.160
03	1.05	0.340	0.410	0.750	0.410	0.160	1.05	2.58	2.15	0.750	0.160	0.160
04	0.750	0.240	0.410	0.750	0.410	0.160	1.05	2.58	2.15	0.750	0.160	0.160
05	0.750	0.240	0.410	0.750	0.410	0.160	1.05	2.58	2.15	0.750	0.160	0.160
06	0.520	0.240	0.410	0.750	0.410	0.160	1.05	2.58	2.15	0.630	0.160	0.160
07	0.520	0.240	0.410	0.750	0.410	0.100	1.20	2.58	1.95	0.630	0.160	0.160
08	0.520	0.240	0.410	0.750	0.890	0.100	1.20	2.58	1.95	0.630	0.160	0.160
09	0.520	0.240	0.410	0.750	0.890	0.160	1.20	2.58	1.95	0.630	0.160	0.160
10	0.520	0.240	0.410	0.750	0.750	0.160	1.20	2.58	1.74	0.630	0.160	0.160
11	0.520	0.240	0.410	0.750	1.05	0.160	1.20	2.58	1.74	0.630	0.160	0.160
12	0.520	0.240	0.410	0.750	1.05	0.100	1.20	2.58	1.74	0.630	0.160	0.160
13	0.520	0.240	0.410	0.750	0.890	0.890	1.20	2.58	1.54	0.630	0.160	0.160
14	0.520	0.240	0.520	0.750	0.890	1.20	1.20	2.58	1.54	0.630	0.160	0.160
15	0.520	0.240	0.520	0.750	0.750	1.05	1.54	2.58	1.54	0.630	0.160	0.160
16	0.520	0.160	0.520	0.750	0.750	1.05	1.95	2.58	1.37	0.520	0.160	0.160
17	0.410	0.160	0.520	0.750	0.750	1.05	1.74	2.58	1.37	0.520	0.160	0.160
18	0.410	0.520	2.35	0.750	0.630	1.05	2.15	2.58	1.20	0.520	0.160	0.160
19	0.410	0.630	5.50	0.750	0.630	1.05	1.95	2.58	1.20	0.520	0.240	0.160
20	0.410	0.630	3.90	5.15	0.630	1.05	2.15	2.58	1.20	0.520	0.160	0.160
21	0.410	0.630	3.05	6.30	0.520	0.750	2.15	2.35	1.20	0.520	0.160	0.160
22	0.410	0.630	2.35	3.90	0.520	0.750	2.15	2.35	1.20	0.520	0.160	0.160
23	0.410	0.630	1.95	2.35	0.410	0.750	2.35	2.35	1.05	0.520	0.160	0.160
24	0.410	0.520	0.750	1.74	0.410	0.750	2.15	2.35	0.890	0.520	0.160	0.160
25	0.340	0.520	0.750	1.20	0.410	0.890	2.15	2.35	0.890	0.520	0.160	0.160
26	0.340	0.520	0.750	0.750	0.410	0.890	2.15	2.35	0.890	0.520	0.050	0.240
27	0.340	0.520	0.750	0.520	0.410	1.05	2.15	2.35	0.890	0.520	0.050	0.240
28	0.340	0.520	0.750	0.520	0.340	1.05	2.35	2.35	0.890	0.410	0.050	0.240
29	0.340	0.520	0.750	0.520	-----	0.890	2.35	2.15	0.890	0.410	0.050	0.160
30	0.340	0.520	0.750	0.520	-----	1.05	2.35	2.15	0.750	0.410	0.050	0.160
31	0.340	-----	0.750	0.520	-----	1.05	-----	2.15	-----	0.410	0.160	-----
Maks.	2.82	1.95	6.70	7.10	1.20	1.54	2.58	2.58	2.15	0.750	0.240	0.240
Min.	0.240	0.160	0.410	0.520	0.340	0.100	1.05	2.15	0.750	0.410	0.050	0.160
Ortalama	0.474	0.384	1.06	1.23	0.602	0.651	1.66	2.48	1.48	0.578	0.145	0.168
LT/SN/Km2	10.5	8.51	23.4	27.3	13.3	14.4	36.7	54.9	32.8	12.8	3.21	3.72
AKIM mm.	28.1	22.1	62.6	73.2	32.2	38.6	95.0	147.	85.1	34.3	8.59	9.64
MİL. M3	1.27	0.996	2.83	3.30	1.46	1.74	4.29	6.64	3.84	1.55	0.388	0.435

SU YILI (2006) YILLIK TOPLAM AKIM 28.74 MİLYON M3 636 MM. 20.2 LT/SN/Km2

08. Bati Akdeniz Havzasi

D08A079 AKSU D. ÇAMKÖY

YERİ : **BURDUR ÇAVDIR YOLUNU TAKİBEN DENİZLİ ACIPAYAM YOLUNA SAPILIR. BÜYÜKALAN KÖYÜNÜ GEÇTİKTEN SONRA AKSU DERESİ YOLUNA SAPILIR 2 KM SONRA İSTASYONA VARILIR. HARİTA PAFTA NO: N23-A4 29°35'29" Doğu - 37°16'42" Kuzey**

YAĞIŞ ALANI : **117,40 km2** **YAKLAŞIK KOT : 1020 m**

GÖZLEM SÜRESİ : **01.10.1977 - 30.09.2006**

ORTALAMA AKIMLAR : **Gözlem süresinde 0.536 m3/sn. (25 Yıllık) 2006 Su yılında 0.251 m3/sn.**

ANLIK EN ÇOK VE EN AZ AKIMLAR:

2006 Su yılında anlık ençok akım	:	**1.56**	**m3/sn**	**07.04.2006**
2006 Su yılında anlık enaz akım	:	**0.000**	**m3/sn**	**27.06.2006**
Gözlem süresinde anlık ençok akım	:	**100.**	**m3/sn**	**08.09.1985**
Gözlem süresinde anlık enaz akım	:	**0.000**	**m3/sn**	**01.10.1977**

İstasyon için kullanılmış anahtar bulunamadı.

Akımlar 01 Ekim 2005 'den 30 Eylül 2006' a kadar m3/sn olarak

Gün	Ekim	Kasım	Aralık	Ocak	Şubat	Mart	Nisan	Mayıs	Haziran	Temmuz	Ağustos	Eylül
01	0.420	0.002	0.345	0.285	0.220	0.663	0.856	0.036	0.002	KURU	KURU	KURU
02	0.663	0.002	0.345	0.285	0.285	0.663	0.745	0.036	0.002	KURU	KURU	KURU
03	0.285	0.002	0.345	0.285	0.285	0.663	0.745	0.036	0.002	KURU	KURU	KURU
04	0.220	0.002	0.345	0.285	0.285	0.663	0.856	0.036	0.002	KURU	KURU	KURU
05	0.220	0.002	0.345	0.285	0.345	0.663	1.19	0.036	0.002	KURU	KURU	KURU
06	0.002	0.002	0.345	0.220	0.345	0.663	1.43	0.036	0.002	KURU	KURU	KURU
07	0.002	0.002	0.345	0.124	0.345	0.575	1.56	0.036	0.002	KURU	KURU	KURU
08	0.002	0.002	0.345	0.124	0.420	0.575	1.56	0.036	0.002	KURU	KURU	KURU
09	0.002	0.036	0.345	0.088	0.420	0.663	1.56	0.036	0.002	KURU	KURU	KURU
10	0.002	0.088	0.345	0.124	0.420	0.663	1.56	0.036	0.002	KURU	KURU	KURU
11	0.002	0.088	0.345	0.124	0.420	0.663	1.43	0.036	0.006	KURU	KURU	KURU
12	0.002	0.088	0.345	0.124	0.420	0.575	1.19	0.036	0.006	KURU	KURU	KURU
13	0.002	0.036	0.285	0.170	0.420	0.663	0.856	0.036	0.006	KURU	KURU	KURU
14	0.002	0.023	0.285	0.124	0.575	1.08	0.745	0.036	0.006	KURU	KURU	KURU
15	0.002	0.023	0.285	0.088	0.575	1.19	0.745	0.036	0.006	KURU	KURU	KURU
16	0.002	0.036	0.285	0.088	0.575	1.19	0.745	0.036	0.013	KURU	KURU	KURU
17	0.002	0.058	0.285	0.124	0.575	1.08	0.745	0.036	0.013	KURU	KURU	KURU
18	0.002	0.575	0.285	0.124	0.575	1.08	0.745	0.036	0.006	KURU	KURU	KURU
19	0.002	0.490	0.285	0.124	0.575	0.967	0.745	0.036	0.006	KURU	KURU	KURU
20	0.002	0.745	0.285	0.124	0.575	0.967	0.745	0.023	0.006	KURU	KURU	KURU
21	0.002	0.420	0.285	0.124	0.575	1.08	0.745	0.013	0.006	KURU	KURU	KURU
22	0.002	0.345	0.285	0.170	0.575	1.08	0.745	0.006	0.002	KURU	KURU	KURU
23	0.002	0.345	0.345	0.170	0.575	1.08	0.745	0.013	0.002	KURU	KURU	KURU
24	0.002	0.345	0.285	0.170	0.575	1.08	0.745	0.006	0.002	KURU	KURU	KURU
25	0.002	0.345	0.285	0.170	0.575	1.30	0.745	0.006	KURU	KURU	KURU	KURU
26	0.002	0.345	0.170	0.220	0.575	1.08	0.745	0.006	KURU	KURU	KURU	KURU
27	0.002	0.345	0.170	0.220	0.663	1.08	0.575	0.006	KURU	KURU	KURU	KURU
28	0.002	0.345	0.220	0.220	0.663	1.08	0.490	0.006	KURU	KURU	KURU	KURU
29	0.002	0.345	0.285	0.220	-----	1.08	0.490	0.006	KURU	KURU	KURU	KURU
30	0.002	0.345	0.285	0.220	-----	0.967	0.420	0.006	KURU	KURU	KURU	KURU
31	0.002	-----	0.285	0.220	-----	0.967	-----	0.006	-----	KURU	KURU	-----
Maks.	0.663	0.745	0.345	0.285	0.663	1.30	1.56	0.036	0.013	KURU	KURU	KURU
Min.	0.002	0.002	0.170	0.088	0.220	0.575	0.420	0.006	KURU	KURU	KURU	KURU
Ortalama	0.060	0.194	0.301	0.176	0.480	0.896	0.907	0.025	0.004	KURU	KURU	KURU
LT/SN/Km2	0.511	1.65	2.56	1.50	4.09	7.63	7.72	0.216	0.030	0.000	0.000	0.000
AKIM mm.	1.37	4.29	6.86	4.01	9.88	20.4	20.0	0.579	0.078	0.000	0.000	0.000
MİL. M3	0.161	0.503	0.805	0.470	1.16	2.40	2.35	0.068	0.009	0.000	0.000	0.000

SU YILI (2006) YILLIK TOPLAM AKIM 7.93 MİLYON M3 68 MM. 2.1 LT/SN/Km2

08. Bati Akdeniz Havzasi

D08A081 ARSLANLI Ç. SORKUN KÖP.

YERİ : **BURDUR GÖLHİSARA YOLUNU TAKİBEN GÖLHİSARA VARMADAN SORKUN KÖYÜ YOLUNA SAPILIR. İSTASYON SORKUN KÖPRÜSÜ ÜZERİNDEDİR. HARİTA PAFTA NO: N23-D1**
29°35'20" Doğu - 37°9'7" Kuzey

YAĞIŞ ALANI : **840,30 km2** **YAKLAŞIK KOT : 956 m**

GÖZLEM SÜRESİ : **11.04.1977 - 30.09.2006**

ORTALAMA AKIMLAR : **Gözlem süresinde 1.144 m3/sn. (27 Yıllık) 2006 Su yılında 0.307 m3/sn.**

ANLIK EN ÇOK VE EN AZ AKIMLAR:

2006 Su yılında anlık ençok akım	:	**0.980**	**m3/sn**	**14.03.2006**
2006 Su yılında anlık enaz akım	:	**0.000**	**m3/sn**	**23.05.2006**
Gözlem süresinde anlık ençok akım	:	**55.0**	**m3/sn**	**31.05.1979**
Gözlem süresinde anlık enaz akım	:	**0.000**	**m3/sn**	**11.10.1977**

5. Anahtar Eğrisi (Seviyeler cm olarak)

Seviye	Akım	Seviye	Akım	Seviye	Akım	Seviye	Akım
1	0.000	11	0.007	51	4.5	101	20.0
3	0.000	13	0.019	61	7.2	111	22.0
5	0.000	21	0.210	71	10.0	121	24.0
7	0.000	31	0.980	81	13.5	131	26.0
9	0.002	41	2.4	91	17.0	161	32.0

Akımlar 01 Ekim 2005 'den 30 Eylül 2006' a kadar m3/sn olarak

Gün	Ekim	Kasım	Aralık	Ocak	Şubat	Mart	Nisan	Mayıs	Haziran	Temmuz	Ağustos	Eylül
01	0.441	0.287	0.441	0.441	0.441	0.518	0.595	0.595	0.002	KURU	KURU	KURU
02	0.150	0.287	0.441	0.518	0.518	0.672	0.595	0.595	0.004	KURU	KURU	KURU
03	0.150	0.364	0.441	0.518	0.518	0.672	0.595	0.595	0.120	KURU	KURU	KURU
04	0.150	0.441	0.441	0.518	0.518	0.672	0.595	0.595	0.046	KURU	KURU	KURU
05	0.210	0.364	0.441	0.441	0.672	0.518	0.595	0.518	0.033	KURU	KURU	KURU
06	0.210	0.364	0.441	0.441	0.672	0.518	0.595	0.518	0.046	KURU	KURU	KURU
07	0.210	0.364	0.441	0.441	0.672	0.518	0.595	0.210	0.090	KURU	KURU	KURU
08	0.364	0.364	0.441	0.441	0.672	0.518	0.595	0.210	0.033	KURU	KURU	KURU
09	0.518	0.364	0.441	0.441	0.595	0.595	0.672	0.210	0.180	KURU	KURU	KURU
10	0.518	0.364	0.441	0.441	0.595	0.595	0.672	0.180	0.120	KURU	KURU	KURU
11	0.364	0.364	0.441	0.441	0.595	0.595	0.672	0.180	0.120	KURU	KURU	KURU
12	0.364	0.364	0.441	0.441	0.595	0.595	0.672	0.150	0.033	KURU	KURU	KURU
13	0.364	0.364	0.441	0.441	0.441	0.595	0.672	0.150	KURU	KURU	KURU	KURU
14	0.364	0.441	0.441	0.441	0.441	0.980	0.672	0.019	KURU	KURU	KURU	KURU
15	0.287	0.441	0.441	0.441	0.441	0.903	0.672	0.012	KURU	KURU	KURU	KURU
16	0.364	0.441	0.441	0.441	0.672	0.749	0.595	0.007	KURU	KURU	KURU	KURU
17	0.518	0.595	0.441	0.441	0.672	0.749	0.595	0.007	KURU	KURU	KURU	KURU
18	0.518	0.595	0.441	0.441	0.672	0.749	0.595	0.004	KURU	KURU	KURU	KURU
19	0.518	0.595	0.441	0.441	0.672	0.672	0.595	0.004	KURU	KURU	KURU	KURU
20	0.441	0.595	0.441	0.441	0.672	0.672	0.595	0.002	KURU	KURU	KURU	KURU
21	0.364	0.595	0.441	0.441	0.672	0.595	0.595	KURU	KURU	KURU	KURU	KURU
22	0.287	0.518	0.441	0.441	0.672	0.595	0.595	KURU	KURU	KURU	KURU	KURU
23	0.364	0.518	0.441	0.441	0.595	0.595	0.595	KURU	KURU	KURU	KURU	KURU
24	0.287	0.518	0.441	0.441	0.595	0.595	0.595	KURU	KURU	KURU	KURU	KURU
25	0.287	0.518	0.441	0.441	0.595	0.595	0.595	KURU	KURU	KURU	KURU	KURU
26	0.364	0.441	0.441	0.441	0.595	0.595	0.595	KURU	KURU	KURU	KURU	KURU
27	0.364	0.441	0.441	0.441	0.518	0.518	0.595	0.364	KURU	KURU	KURU	KURU
28	0.364	0.441	0.441	0.441	0.518	0.518	0.595	0.120	KURU	KURU	KURU	KURU
29	0.364	0.441	0.441	0.441	-----	0.595	0.595	0.046	KURU	KURU	KURU	KURU
30	0.364	0.441	0.441	0.441	-----	0.595	0.595	KURU	KURU	KURU	KURU	KURU
31	0.364	-----	0.441	0.441	-----	0.595	-----	KURU	-----	KURU	KURU	-----
Maks.	0.518	0.595	0.441	0.518	0.672	0.980	0.672	0.595	0.180	KURU	KURU	KURU
Min.	0.150	0.287	0.441	0.441	0.441	0.518	0.595	KURU	KURU	KURU	KURU	KURU
Ortalama	0.348	0.441	0.441	0.448	0.590	0.627	0.613	0.171	0.028	KURU	KURU	KURU
LT/SN/Km2	0.414	0.525	0.525	0.534	0.702	0.747	0.729	0.203	0.033	0.000	0.000	0.000
AKIM mm.	1.11	1.36	1.41	1.43	1.70	2.00	1.89	0.544	0.085	0.000	0.000	0.000
MİL. M3	0.933	1.14	1.18	1.20	1.43	1.68	1.59	0.457	0.071	0.000	0.000	0.000

SU YILI (2006) YILLIK TOPLAM AKIM 9.68 MİLYON M3 12 MM. 0.4 LT/SN/Km2

08. Bati Akdeniz Havzasi

D08A083 DARGAZ D. LENGÜME

YERİ : **ELMALI-GÖMBE YOLUNUN 30 KM.SİNDEKI LENGÜME OVASINDAN SAĞA AYRILAN YOLUN 8 KM. ILERISINDEDIR (PAFTA P22-B2)**
29°29'34" Doğu - 36°24'0" Kuzey

YAĞIŞ ALANI : **93,60 km2** **YAKLAŞIK KOT : 815 m**

GÖZLEM SÜRESİ : **01.10.1978 - 30.09.2006**

ORTALAMA AKIMLAR : **Gözlem süresinde 0.943 m3/sn. (28 Yıllık) 2006 Su yılında 0.319 m3/sn.**

ANLIK EN ÇOK VE EN AZ AKIMLAR:

2006 Su yılında anlık ençok akım	:	**13.5**	**m3/sn**	**14.03.2006**
2006 Su yılında anlık enaz akım	:	**0.000**	**m3/sn**	**01.10.2005**
Gözlem süresinde anlık ençok akım	:	**57.2**	**m3/sn**	**22.01.2004**
Gözlem süresinde anlık enaz akım	:	**0.000**	**m3/sn**	**27.05.1982**

Akımlar 01 Ekim 2005 'den 30 Eylül 2006' a kadar m3/sn olarak

Gün	Ekim	Kasım	Aralık	Ocak	Şubat	Mart	Nisan	Mayıs	Haziran	Temmuz	Ağustos	Eylül
01	KURU	0.010	0.148	0.122	0.336	0.595	0.904	0.392	0.071	0.021	KURU	KURU
02	KURU	0.010	0.173	0.122	0.295	0.549	0.816	0.392	0.071	0.021	KURU	KURU
03	KURU	0.018	0.173	0.122	0.255	0.503	0.816	0.392	0.071	0.013	KURU	KURU
04	KURU	0.018	0.173	0.122	0.255	0.503	0.816	0.392	0.071	0.071	KURU	KURU
05	KURU	0.018	0.173	0.122	0.255	0.503	0.729	0.392	0.071	0.122	KURU	KURU
06	0.036	0.018	0.173	0.122	0.447	0.447	0.729	0.392	0.071	0.122	KURU	KURU
07	0.036	0.018	0.173	0.122	1.44	0.447	0.729	0.392	0.071	0.071	KURU	KURU
08	0.036	0.018	0.173	0.122	1.35	0.641	0.729	0.336	0.071	0.047	KURU	KURU
09	0.036	0.018	0.173	0.122	1.08	0.816	0.641	0.295	0.071	0.028	KURU	KURU
10	0.025	0.018	0.173	0.122	1.08	0.595	0.641	0.255	0.071	0.021	KURU	KURU
11	0.100	0.018	0.173	0.122	1.80	0.595	0.729	0.214	0.047	0.021	KURU	KURU
12	0.046	0.018	0.173	0.122	3.36	0.595	0.595	0.214	0.047	KURU	KURU	KURU
13	0.036	0.018	0.173	0.122	1.80	3.22	0.595	0.255	0.047	KURU	KURU	KURU
14	0.025	0.018	0.173	0.122	1.35	6.28	0.595	0.214	0.047	KURU	KURU	KURU
15	0.025	0.018	0.295	0.122	1.08	3.22	0.595	0.214	0.028	KURU	KURU	KURU
16	0.025	0.018	0.255	0.122	0.904	2.50	0.641	0.214	0.028	KURU	KURU	KURU
17	0.025	0.018	0.255	0.122	0.816	1.94	0.595	0.255	0.028	KURU	KURU	KURU
18	0.018	0.046	1.44	0.097	1.08	2.07	0.549	0.214	0.028	KURU	KURU	KURU
19	0.018	0.086	1.62	0.071	0.904	2.21	0.549	0.214	0.021	KURU	KURU	KURU
20	0.018	0.135	0.336	0.255	0.729	1.71	0.549	0.255	0.021	KURU	KURU	KURU
21	0.018	0.295	0.214	0.173	0.641	1.62	0.549	0.214	0.021	KURU	KURU	KURU
22	0.018	0.214	0.148	0.173	0.641	1.53	0.503	0.214	0.021	KURU	KURU	KURU
23	0.018	0.173	0.148	0.816	0.595	1.44	0.549	0.173	0.021	KURU	KURU	KURU
24	0.018	0.173	0.097	0.595	0.595	1.35	0.503	0.148	0.021	KURU	KURU	KURU
25	0.018	0.148	0.047	1.71	0.595	1.26	0.503	0.122	0.021	KURU	KURU	KURU
26	0.018	0.148	0.097	0.816	0.549	1.17	0.503	0.122	0.013	KURU	KURU	KURU
27	0.018	0.148	0.122	0.549	0.549	1.17	0.503	0.122	0.071	KURU	KURU	KURU
28	0.018	0.148	0.148	0.503	0.549	1.08	0.503	0.097	0.028	KURU	KURU	KURU
29	0.010	0.148	0.148	0.392	-----	0.994	0.503	0.097	0.028	KURU	KURU	KURU
30	0.010	0.148	0.148	0.336	-----	0.904	0.447	0.097	0.028	KURU	KURU	KURU
31	0.010	-----	0.122	0.336	-----	0.994	-----	0.097	-----	KURU	KURU	-----
Maks.	3.80	4.40	8.10	3.08	5.01	13.5	0.994	0.447	0.904	0.122	KURU	0.549
Min.	KURU	0.010	0.021	0.047	0.255	0.447	0.392	0.071	0.013	KURU	KURU	KURU
Ortalama	0.022	0.077	0.259	0.287	0.905	1.40	0.620	0.239	0.044	0.018	KURU	KURU
LT/SN/Km2	0.234	0.819	2.77	3.07	9.66	15.0	6.63	2.55	0.472	0.192	0.000	0.000
AKIM mm.	0.627	2.12	7.42	8.21	23.4	40.1	17.2	6.83	1.22	0.515	0.000	0.000
MİL. M3	0.059	0.199	0.694	0.769	2.19	3.75	1.61	0.639	0.114	0.048	0.000	0.000

SU YILI (2006) YILLIK TOPLAM AKIM 10.07 MİLYON M3 108 MM. 3.4 LT/SN/Km2

08. Bati Akdeniz Havzasi

D08A084 DEGİRMEN D. SODAKÖY

YERİ : **MUĞLA KALE KARAYOLUNUN 11. KM.SİNDEKİ SODAKÖY'ÜN GÜNEYİNDEKİ ABDULLAH PINARI MEVKİİNDEDİR**

28°27'21" Doğu - 37°10'46" Kuzey

YAĞIŞ ALANI : **17,13 km2** **YAKLAŞIK KOT : 665 m**

GÖZLEM SÜRESİ : **01.02.1980 - 30.09.2006**

ORTALAMA AKIMLAR : **Gözlem süresinde 0.096 m3/sn. (27 Yıllık) 2006 Su yılında 0.061 m3/sn.**

ANLIK EN ÇOK VE EN AZ AKIMLAR:

2006 Su yılında anlık ençok akım	:	**8.60**	**m3/sn**	**06.02.2006**
2006 Su yılında anlık enaz akım	:	**0.000**	**m3/sn**	**01.10.2005**
Gözlem süresinde anlık ençok akım	:	**43.4**	**m3/sn**	**13.12.1990**
Gözlem süresinde anlık enaz akım	:	**0.000**	**m3/sn**	**01.07.1980**

Akımlar 01 Ekim 2005 'den 30 Eylül 2006' a kadar m3/sn olarak

Gün	Ekim	Kasım	Aralık	Ocak	Şubat	Mart	Nisan	Mayıs	Haziran	Temmuz	Ağustos	Eylül
01	KURU	KURU	KURU	KURU	0.006	0.001	0.038	0.003	KURU	KURU	KURU	KURU
02	KURU	KURU	KURU	KURU	0.011	0.001	0.038	0.003	KURU	KURU	KURU	KURU
03	KURU	KURU	KURU	KURU	0.038	0.001	0.038	0.003	KURU	KURU	KURU	KURU
04	KURU	KURU	KURU	KURU	0.038	0.001	0.038	0.003	KURU	KURU	KURU	KURU
05	KURU	KURU	KURU	0.001	0.038	0.001	0.038	0.001	KURU	KURU	KURU	KURU
06	KURU	KURU	KURU	0.100	2.30	0.001	0.038	0.001	KURU	KURU	KURU	KURU
07	KURU	KURU	KURU	0.062	0.794	0.003	0.038	0.001	KURU	KURU	KURU	KURU
08	KURU	KURU	KURU	0.062	1.28	0.320	0.038	0.001	KURU	KURU	KURU	KURU
09	KURU	KURU	KURU	0.062	0.440	0.140	0.038	0.001	KURU	KURU	KURU	KURU
10	KURU	KURU	KURU	0.062	0.370	0.062	0.038	KURU	KURU	KURU	KURU	KURU
11	KURU	KURU	KURU	0.062	0.891	0.440	0.038	KURU	KURU	KURU	KURU	KURU
12	KURU	KURU	KURU	0.062	1.09	1.98	0.038	KURU	KURU	KURU	KURU	KURU
13	KURU	KURU	KURU	0.062	0.440	1.87	0.038	KURU	KURU	KURU	KURU	KURU
14	KURU	KURU	KURU	0.062	0.320	2.08	0.038	KURU	KURU	KURU	KURU	KURU
15	KURU	KURU	KURU	0.062	0.140	0.543	0.020	KURU	KURU	KURU	KURU	KURU
16	KURU	KURU	KURU	0.062	0.062	0.370	0.020	KURU	KURU	KURU	KURU	KURU
17	KURU	KURU	KURU	0.062	0.062	0.270	0.020	KURU	KURU	KURU	KURU	KURU
18	KURU	KURU	KURU	0.062	0.062	0.270	0.020	KURU	KURU	KURU	KURU	KURU
19	KURU	KURU	0.006	0.062	0.062	0.180	0.020	KURU	KURU	KURU	KURU	KURU
20	KURU	KURU	KURU	0.180	0.038	0.140	0.011	KURU	KURU	KURU	KURU	KURU
21	KURU	KURU	KURU	0.003	0.020	0.140	0.011	KURU	KURU	KURU	KURU	KURU
22	KURU	KURU	KURU	0.003	0.003	0.100	0.011	KURU	KURU	KURU	KURU	KURU
23	KURU	KURU	KURU	0.062	0.001	0.062	0.011	KURU	KURU	KURU	KURU	KURU
24	KURU	KURU	KURU	1.09	0.001	0.062	0.011	KURU	KURU	KURU	KURU	KURU
25	KURU	KURU	KURU	0.988	0.001	0.062	0.006	KURU	KURU	KURU	KURU	KURU
26	KURU	KURU	KURU	0.230	0.001	0.038	0.006	KURU	KURU	KURU	KURU	KURU
27	KURU	KURU	KURU	0.100	0.001	0.038	0.006	KURU	KURU	KURU	KURU	KURU
28	KURU	KURU	KURU	0.006	0.001	0.038	0.006	KURU	KURU	KURU	KURU	KURU
29	KURU	KURU	0.038	0.006	-----	0.038	0.006	KURU	KURU	KURU	KURU	KURU
30	KURU	KURU	0.001	0.006	-----	0.038	0.003	KURU	KURU	KURU	KURU	KURU
31	KURU	-----	KURU	0.006	-----	0.038	-----	KURU	-----	KURU	KURU	-----
Maks.	KURU	0.480	1.47	4.25	8.60	6.25	0.180	0.003	KURU	KURU	KURU	KURU
Min.	KURU	KURU	KURU	KURU	0.001	0.001	0.003	KURU	KURU	KURU	KURU	KURU
Ortalama	KURU	KURU	0.001	0.116	0.304	0.301	0.024	0.001	KURU	KURU	KURU	KURU
LT/SN/Km2	0.000	0.000	0.085	6.75	17.7	17.6	1.40	0.032	0.000	0.000	0.000	0.000
AKIM mm.	0.000	0.000	0.227	18.1	42.9	47.0	3.63	0.086	0.000	0.000	0.000	0.000
MİL. M3	0.000	0.000	0.004	0.310	0.735	0.806	0.062	0.001	0.000	0.000	0.000	0.000

SU YILI (2006) YILLIK TOPLAM AKIM 1.92 MİLYON M3 112 MM. 3.6 LT/SN/Km2

08. Bati Akdeniz Havzasi

D08A087 DEĞİRMEN D. KARADAM

YERİ : **MUĞLA-MİLAS ÖREN KARAYOLUNUN 24 KM-SİNDEKİ KARAHİSAR KÖYÜ KÖRÜSÜNÜN MENBASINDADIR**

27°48'38" Doğu - 37°9'49" Kuzey

YAĞIŞ ALANI : **141,00 km2** **YAKLAŞIK KOT : 115 m**

GÖZLEM SÜRESİ : **21.11.1980 - 30.09.2006**

ORTALAMA AKIMLAR : **Gözlem süresinde 0.605 m3/sn. (23 Yıllık) 2006 Su yılında 0.550 m3/sn.**

ANLIK EN ÇOK VE EN AZ AKIMLAR:

2006 Su yılında anlık ençok akım	**:**	**140.**	**m3/sn**	**22.05.2006**
2006 Su yılında anlık enaz akım	**:**	**0.000**	**m3/sn**	**01.10.2005**
Gözlem süresinde anlık ençok akım	**:**	**190.**	**m3/sn**	**01.02.1983**
Gözlem süresinde anlık enaz akım	**:**	**0.000**	**m3/sn**	**19.04.1981**

Akımlar 01 Ekim 2005 'den 30 Eylül 2006' a kadar m3/sn olarak

Gün	Ekim	Kasım	Aralık	Ocak	Şubat	Mart	Nisan	Mayıs	Haziran	Temmuz	Ağustos	Eylül
01	KURU	KURU	0.395	0.350	0.575	1.60	0.888	0.200	0.038	KURU	KURU	KURU
02	2.20	KURU	0.305	0.305	0.530	1.51	0.977	0.200	0.026	KURU	KURU	KURU
03	0.167	KURU	0.395	0.305	0.530	1.16	0.977	0.140	0.032	KURU	KURU	KURU
04	0.167	0.018	0.440	0.260	0.440	1.16	0.888	0.160	0.021	KURU	KURU	KURU
05	0.167	0.010	0.395	0.665	0.485	1.24	0.888	0.140	0.021	KURU	KURU	KURU
06	0.167	0.010	0.395	0.977	1.33	1.24	0.799	0.140	0.021	KURU	KURU	KURU
07	0.122	0.010	0.395	0.665	3.45	1.42	0.799	0.120	0.021	KURU	KURU	KURU
08	0.122	0.010	0.395	0.575	2.15	2.15	0.799	0.100	0.021	KURU	KURU	KURU
09	0.122	0.010	0.395	0.485	1.93	1.93	0.888	0.080	0.010	KURU	KURU	KURU
10	0.122	0.004	0.395	0.395	1.82	1.82	1.07	0.054	0.010	KURU	KURU	KURU
11	0.122	0.006	0.395	0.305	1.93	1.82	0.799	0.054	0.010	KURU	KURU	KURU
12	0.122	0.006	0.350	0.260	1.93	3.60	0.888	0.049	0.004	KURU	KURU	KURU
13	0.059	0.004	0.350	0.240	1.82	13.4	0.888	0.049	0.004	KURU	KURU	KURU
14	0.018	0.002	0.350	0.240	1.82	6.00	0.888	0.049	0.004	KURU	KURU	KURU
15	0.018	0.010	0.888	0.220	1.93	4.36	0.888	0.049	0.003	KURU	KURU	KURU
16	0.014	0.010	0.575	0.220	1.93	2.70	0.888	0.049	KURU	KURU	KURU	KURU
17	0.010	0.014	0.575	0.220	1.93	2.37	0.710	0.049	KURU	KURU	KURU	KURU
18	0.018	1.54	1.33	0.200	1.71	2.15	0.665	0.049	KURU	KURU	KURU	KURU
19	0.018	0.332	11.3	0.220	1.60	1.93	0.620	0.049	KURU	KURU	KURU	KURU
20	0.014	0.821	2.04	0.395	1.51	1.60	0.665	0.049	KURU	KURU	KURU	KURU
21	0.010	0.332	1.42	0.305	2.26	1.42	0.620	0.043	KURU	KURU	KURU	KURU
22	0.010	0.197	0.799	0.260	2.15	1.33	0.575	0.043	KURU	KURU	KURU	KURU
23	0.006	0.197	0.620	0.665	0.710	1.33	0.485	0.043	KURU	KURU	KURU	KURU
24	0.006	0.226	0.575	0.888	0.665	1.33	0.395	0.043	KURU	KURU	KURU	KURU
25	KURU	0.197	0.485	3.45	0.665	1.33	0.305	0.043	KURU	KURU	KURU	0.004
26	0.004	11.3	0.485	1.51	0.710	1.24	0.305	0.043	0.003	KURU	KURU	0.002
27	0.004	1.33	0.440	1.07	1.07	1.16	0.260	0.038	0.015	KURU	KURU	KURU
28	KURU	0.620	0.395	0.888	1.42	1.07	0.240	0.038	0.021	KURU	KURU	KURU
29	KURU	0.440	0.395	0.710	-----	1.07	0.200	0.038	0.004	KURU	KURU	KURU
30	KURU	0.440	0.305	0.620	-----	0.888	0.200	0.032	0.003	KURU	KURU	KURU
31	KURU	-----	0.305	0.575	-----	0.888	-----	0.032	-----	KURU	KURU	-----
Maks.	114.	35.1	31.6	5.80	9.34	96.8	10.0	140.	0.038	KURU	KURU	0.004
Min.	KURU	KURU	0.080	0.120	0.440	0.888	0.200	0.010	KURU	KURU	KURU	KURU
Ortalama	0.123	0.603	0.912	0.595	1.46	2.20	0.682	0.073	0.010	KURU	KURU	0.000
LT/SN/Km2	0.871	4.28	6.47	4.22	10.4	15.6	4.84	0.518	0.069	0.000	0.000	0.001
AKIM mm.	2.33	11.1	17.3	11.3	25.1	41.8	12.5	1.39	0.179	0.000	0.000	0.004
MİL. M3	0.329	1.56	2.44	1.59	3.54	5.89	1.77	0.196	0.025	0.000	0.000	0.001

SU YILI (2006) YILLIK TOPLAM AKIM 17.34 MİLYON M3 123 MM. 3.9 LT/SN/Km2

08. Bati Akdeniz Havzasi

D08A089 KARGI Ç. YANIKLAR

YERİ : **FETHİYE KÖYCEĞİZ KARAYOLUNUN 17KM.SİDEKİ,KARGI KÖYÜNDEN SOLA AYRILAN MADEN YOLUNUN 4.KM-SİNDEDİR.**
29°4'4" Doğu - 36°44'41" Kuzey

YAĞIŞ ALANI : **194,00 km2** **YAKLAŞIK KOT : 97 m**

GÖZLEM SÜRESİ : **15.11.1982 - 30.09.2006**

ORTALAMA AKIMLAR : **Gözlem süresinde 4.437 m3/sn. (22 Yıllık) 2006 Su yılında 4.108 m3/sn.**

ANLIK EN ÇOK VE EN AZ AKIMLAR:

2006 Su yılında anlık ençok akım	:	**49.3**	**m3/sn**	**14.03.2006**
2006 Su yılında anlık enaz akım	:	**2.20**	**m3/sn**	**01.10.2005**
Gözlem süresinde anlık ençok akım	:	**270.**	**m3/sn**	**15.11.1988**
Gözlem süresinde anlık enaz akım	:	**0.200**	**m3/sn**	**27.01.1999**

Akımlar 01 Ekim 2005 'den 30 Eylül 2006' a kadar m3/sn olarak

Gün	Ekim	Kasım	Aralık	Ocak	Şubat	Mart	Nisan	Mayıs	Haziran	Temmuz	Ağustos	Eylül
01	2.39	2.39	3.44	2.57	5.33	7.36	5.44	3.90	2.98	2.75	2.98	2.75
02	6.95	2.39	3.21	2.57	5.33	7.07	5.44	3.90	2.98	2.75	2.98	2.75
03	12.7	2.57	3.44	2.57	5.04	6.78	5.44	3.90	2.98	2.76	2.98	2.75
04	8.35	2.39	3.21	2.57	5.04	6.78	5.44	3.90	2.98	2.75	2.98	2.75
05	2.57	2.57	3.21	2.57	4.75	6.78	5.15	3.90	2.98	2.75	2.98	2.75
06	2.57	2.39	3.21	2.75	5.91	6.49	5.15	3.90	2.98	2.75	2.98	2.75
07	2.57	2.39	3.21	2.75	9.74	6.49	5.15	3.90	2.98	2.75	2.98	2.75
08	2.57	2.39	3.21	2.75	11.4	9.10	4.90	3.90	2.98	2.75	2.98	2.75
09	2.57	2.39	3.21	2.57	8.52	9.10	4.90	3.67	2.98	2.75	2.98	2.75
10	2.39	2.57	3.21	2.39	5.62	7.94	4.90	3.67	3.21	2.75	2.98	2.75
11	2.57	2.57	2.98	2.39	7.07	7.65	4.65	4.15	3.21	2.98	2.98	2.75
12	2.57	2.39	2.98	2.39	19.0	7.65	4.65	4.15	2.98	2.98	2.98	2.75
13	2.57	2.39	2.98	2.39	11.8	10.4	4.65	4.15	2.98	2.98	2.98	2.75
14	2.57	2.57	2.98	2.39	9.42	29.1	4.65	3.90	2.75	2.98	2.98	2.75
15	2.57	2.57	2.98	2.39	6.20	13.9	4.65	3.90	2.75	2.98	2.98	2.75
16	2.39	2.57	2.98	2.39	8.52	9.40	4.40	3.90	2.75	2.98	2.98	2.75
17	2.57	2.75	2.98	2.39	8.23	8.35	4.40	3.90	2.75	2.98	2.98	2.75
18	2.39	4.40	5.73	2.39	9.42	8.00	4.40	3.90	2.75	2.98	2.98	2.75
19	2.39	2.98	7.65	2.39	9.10	7.30	4.15	3.67	2.57	2.98	2.75	2.75
20	2.39	9.40	7.30	7.65	8.52	6.60	4.15	3.44	2.57	2.98	2.75	2.57
21	2.39	5.44	4.15	7.65	8.23	6.31	4.15	3.44	2.57	2.98	2.75	2.57
22	2.57	3.21	3.21	3.67	7.94	6.02	4.15	3.44	2.57	2.98	2.75	2.57
23	2.39	2.98	2.98	3.90	7.65	6.02	4.15	3.44	2.57	2.98	2.75	2.57
24	2.39	2.75	2.75	4.40	7.36	6.02	4.15	3.44	2.57	2.98	2.75	4.56
25	2.57	2.75	2.75	17.2	7.36	6.02	4.15	3.44	2.57	2.98	2.75	2.77
26	2.39	2.57	2.75	11.1	7.65	6.02	3.90	3.44	2.57	2.98	2.75	2.35
27	2.57	2.57	2.57	8.23	7.94	5.73	3.90	3.44	2.75	2.98	2.75	2.35
28	2.39	2.75	2.57	7.07	7.36	5.73	3.90	3.44	2.75	2.98	2.75	2.35
29	2.39	2.98	2.57	6.78	-----	5.73	3.90	3.21	2.75	2.98	2.75	2.35
30	2.39	3.21	2.57	6.20	-----	5.73	3.90	2.98	2.75	2.98	2.75	2.35
31	2.39	-----	2.57	5.62	-----	5.44	-----	2.98	-----	2.98	2.75	-----
Maks.	15.7	11.2	7.65	35.0	24.8	49.3	5.73	4.65	3.44	3.44	3.90	15.4
Min.	2.20	2.20	2.39	2.20	4.51	5.44	3.67	2.98	2.39	2.57	2.57	2.20
Ortalama	3.14	3.01	3.40	4.42	8.05	7.97	4.56	3.69	2.82	2.91	2.88	2.72
LT/SN/Km2	16.2	15.5	17.5	22.8	41.5	41.1	23.5	19.0	14.5	15.0	14.9	14.0
AKIM mm.	43.4	40.2	47.0	61.0	100.	110.	61.0	50.9	37.6	40.1	39.8	36.3
MİL. M3	8.42	7.80	9.12	11.8	19.5	21.3	11.8	9.87	7.30	7.78	7.72	7.05

SU YILI (2006) YILLIK TOPLAM AKIM 129.46 MİLYON M3 667 MM. 21.2 LT/SN/Km2

08. Bati Akdeniz Havzasi

D08A091 ESEN Ç. ÖRENKÖY REG.

YERİ : **FETHİYE-KEMER-SEYDİLER-ÖREN YOLU ÜZERİNDEKİ ÖREN KÖPRÜSÜNÜN 1,5 KM. MEBASINDADIR**

29°23'47" Doğu - 36°45'45" Kuzey

YAĞIŞ ALANI : **802,00 km2** **YAKLAŞIK KOT : 207 m**

GÖZLEM SÜRESİ : **06.11.1982 - 30.09.2006**

ORTALAMA AKIMLAR : **Gözlem süresinde 14.358 m3/sn. (22 Yıllık) 2006 Su yılında 8.370 m3/sn.**

ANLIK EN ÇOK VE EN AZ AKIMLAR:

2006 Su yılında anlık ençok akım	:	**90.1**	**m3/sn**	**11.02.2006**
2006 Su yılında anlık enaz akım	:	**0.128**	**m3/sn**	**09.10.2005**
Gözlem süresinde anlık ençok akım	:	**440.**	**m3/sn**	**15.11.1988**
Gözlem süresinde anlık enaz akım	:	**0.128**	**m3/sn**	**09.10.2005**

Akımlar 01 Ekim 2005 'den 30 Eylül 2006' a kadar m3/sn olarak

Gün	Ekim	Kasım	Aralık	Ocak	Şubat	Mart	Nisan	Mayıs	Haziran	Temmuz	Ağustos	Eylül
01	5.60	2.20	3.40	3.80	6.80	11.7	20.4	13.1	5.60	5.00	4.20	6.20
02	5.60	2.20	4.20	3.80	6.20	11.0	19.6	13.1	5.60	6.20	4.20	6.20
03	5.60	3.40	3.80	3.40	5.60	11.0	18.8	12.4	5.60	6.80	4.60	6.20
04	5.00	3.80	3.40	3.80	5.60	11.0	18.8	11.7	5.60	5.60	4.20	6.20
05	5.00	3.80	3.40	3.80	5.00	11.0	18.0	12.4	5.00	8.60	4.20	6.80
06	3.80	3.00	3.80	3.80	5.00	10.4	17.3	11.7	5.00	7.40	4.20	6.20
07	3.40	3.00	3.40	3.80	11.7	9.80	17.3	11.0	5.00	6.20	3.80	3.80
08	3.40	3.00	4.60	3.80	13.1	13.1	17.3	11.0	4.60	6.20	3.80	8.60
09	2.60	3.00	5.00	3.80	11.0	13.8	17.3	10.4	4.20	5.60	3.40	6.80
10	2.60	2.60	5.60	3.80	11.0	11.7	16.6	9.80	4.60	5.00	3.40	6.20
11	2.60	2.60	5.00	4.20	62.6	11.0	16.6	9.20	4.20	5.00	3.00	6.80
12	2.60	3.00	4.60	3.80	60.4	11.0	16.6	9.80	4.60	4.60	3.40	6.20
13	1.80	2.60	5.00	3.80	29.6	15.2	17.3	9.20	5.00	4.60	3.80	6.20
14	2.60	3.40	5.00	3.80	20.4	38.0	16.6	8.60	5.00	4.60	3.80	6.80
15	2.20	3.80	5.60	3.40	16.6	30.5	20.4	8.00	5.60	4.60	3.80	6.20
16	2.20	4.20	5.60	3.40	13.8	27.8	27.8	8.00	5.00	4.60	3.80	6.20
17	3.00	3.80	5.00	3.00	13.1	24.4	21.2	8.00	4.60	3.80	3.80	6.80
18	3.00	4.60	9.80	3.00	15.2	23.6	18.8	8.00	4.60	4.60	4.20	7.40
19	3.00	5.60	16.6	3.40	15.2	22.0	17.3	8.00	4.20	3.80	5.60	7.40
20	3.40	11.7	11.7	18.0	13.8	21.2	16.6	7.40	3.80	3.40	7.40	7.40
21	3.00	7.40	8.00	8.00	13.1	21.2	16.6	6.80	3.80	3.40	6.20	8.00
22	3.40	6.20	6.20	6.80	12.4	20.4	15.2	6.80	4.20	3.40	6.80	8.00
23	2.60	4.60	5.00	7.40	12.4	20.4	18.0	8.00	4.60	3.40	7.40	8.00
24	2.60	4.20	5.60	8.00	12.4	21.2	19.6	7.40	4.60	4.60	7.40	8.00
25	3.00	4.20	5.00	15.2	12.4	22.0	15.9	6.80	4.60	3.80	6.80	8.60
26	3.40	4.20	3.80	13.1	12.4	21.2	15.2	6.20	4.20	3.40	7.40	8.60
27	2.60	3.80	4.20	9.80	11.7	19.6	13.8	6.20	6.80	3.40	6.80	8.60
28	2.60	3.80	4.20	8.00	11.0	21.2	13.8	6.20	6.80	3.80	6.80	9.20
29	3.40	4.20	4.20	6.80	-----	20.4	15.2	6.20	7.40	4.20	6.20	9.80
30	2.60	3.40	3.80	6.80	-----	19.6	13.8	5.60	6.80	3.80	6.80	10.4
31	2.60	-----	3.80	7.40	-----	20.4	-----	5.60	-----	4.20	5.60	-----
Maks.	11.0	17.3	24.4	33.2	90.1	57.1	37.0	21.2	10.4	15.2	11.0	16.6
Min.	0.128	0.182	0.140	0.245	0.415	3.40	13.1	0.329	0.224	0.287	0.308	0.350
Ortalama	3.25	4.04	5.43	5.96	15.7	18.3	17.6	8.79	5.04	4.76	5.06	7.26
LT/SN/Km2	4.05	5.04	6.77	7.43	19.6	22.8	21.9	11.0	6.28	5.94	6.31	9.05
AKIM mm.	10.9	13.1	18.1	19.9	47.3	61.1	56.8	29.4	16.3	15.9	16.9	23.5
MİL. M3	8.71	10.5	14.5	16.0	38.0	49.0	45.6	23.6	13.1	12.8	13.5	18.8

SU YILI (2006) YILLIK TOPLAM AKIM 264.11 MİLYON M3 329 MM. 10.4 LT/SN/Km2

08. Bati Akdeniz Havzasi

D08A092 BAYIR Ç. GÖKÇEBURUN

YERİ : **BURDUR'UN ÇAVDIR İLÇESİNE 15 KM MESAFEDEKİ BAYIR KÖYÜNÜN GİRİŞİNDEKİ KÖPRÜSÜNDEDİR**
HARİTA PAFTA NO: N23-D3
29°42'45" Doğu - 37°6'10" Kuzey

YAĞIŞ ALANI : **626,00 km2** **YAKLAŞIK KOT : 1045 m**

GÖZLEM SÜRESİ : **01.10.1983 - 30.09.2006**

ORTALAMA AKIMLAR : **Gözlem süresinde 0.703 m3/sn. (20 Yıllık) 2006 Su yılında 0.159 m3/sn.**

ANLIK EN ÇOK VE EN AZ AKIMLAR:

2006 Su yılında anlık ençok akım	:	**0.900**	**m3/sn**	**05.06.2006**
2006 Su yılında anlık enaz akım	:	**0.009**	**m3/sn**	**12.03.2006**
Gözlem süresinde anlık ençok akım	:	**30.0**	**m3/sn**	**09.01.1987**
Gözlem süresinde anlık enaz akım	:	**0.000**	**m3/sn**	**22.08.1987**

9. Anahtar Eğrisi (Seviyeler cm olarak)

Seviye	Akım	Seviye	Akım	Seviye	Akım	Seviye	Akım
8	0.001	25	0.360	60	5.6	110	25.0
9	0.002	30	0.680	70	8.6	122	29.7
10	0.004	35	1.1	80	12.0		
15	0.033	40	1.7	90	15.5		
20	0.130	50	3.3	100	20.0		

Akımlar 01 Ekim 2005 'den 30 Eylül 2006' a kadar m3/sn olarak

Gün	Ekim	Kasım	Aralık	Ocak	Şubat	Mart	Nisan	Mayıs	Haziran	Temmuz	Ağustos	Eylül
01	0.325	0.043	0.038	0.029	0.029	0.018	0.066	0.107	0.400	0.250	0.275	0.300
02	0.222	0.043	0.038	0.029	0.029	0.018	0.070	0.098	0.425	0.250	0.300	0.300
03	0.073	0.043	0.038	0.029	0.029	0.018	0.080	0.095	0.700	0.250	0.300	0.275
04	0.070	0.043	0.038	0.029	0.029	0.018	0.098	0.095	0.800	0.250	0.300	0.325
05	0.070	0.043	0.038	0.029	0.029	0.018	0.107	0.092	0.900	0.250	0.300	0.325
06	0.068	0.043	0.038	0.029	0.029	0.018	0.107	0.092	0.900	0.241	0.300	0.325
07	0.068	0.043	0.038	0.029	0.027	0.019	0.101	0.089	0.900	0.241	0.300	0.375
08	0.066	0.042	0.038	0.029	0.027	0.014	0.098	0.092	0.900	0.241	0.300	0.400
09	0.066	0.042	0.037	0.029	0.027	0.015	0.098	0.092	0.900	0.241	0.300	0.350
10	0.066	0.042	0.037	0.029	0.026	0.013	0.098	0.089	0.900	0.241	0.325	0.350
11	0.066	0.042	0.035	0.029	0.026	0.011	0.089	0.086	0.900	0.241	0.325	0.350
12	0.066	0.042	0.035	0.029	0.026	0.009	0.089	0.089	0.700	0.241	0.325	0.325
13	0.063	0.042	0.034	0.029	0.026	0.018	0.095	0.101	0.375	0.241	0.400	0.250
14	0.063	0.042	0.034	0.029	0.025	0.155	0.115	0.110	0.350	0.241	0.450	0.250
15	0.063	0.042	0.034	0.029	0.025	0.089	0.104	0.133	0.300	0.241	0.450	0.275
16	0.061	0.042	0.034	0.029	0.024	0.073	0.101	0.137	0.300	0.241	0.500	0.275
17	0.061	0.040	0.034	0.029	0.024	0.061	0.098	0.146	0.300	0.241	0.425	0.300
18	0.056	0.040	0.034	0.029	0.024	0.054	0.098	0.155	0.300	0.241	0.375	0.325
19	0.058	0.040	0.034	0.029	0.024	0.049	0.098	0.174	0.250	0.241	0.375	0.325
20	0.058	0.040	0.034	0.029	0.022	0.045	0.095	0.203	0.250	0.241	0.350	0.325
21	0.056	0.040	0.032	0.029	0.022	0.043	0.095	0.231	0.250	0.250	0.350	0.300
22	0.054	0.040	0.031	0.029	0.022	0.042	0.101	0.231	0.250	0.250	0.425	0.241
23	0.052	0.040	0.030	0.029	0.019	0.040	0.098	0.250	0.250	0.250	0.375	0.231
24	0.049	0.038	0.029	0.029	0.019	0.042	0.098	0.250	0.250	0.250	0.350	0.241
25	0.049	0.038	0.029	0.029	0.019	0.047	0.095	0.300	0.250	0.275	0.350	0.241
26	0.049	0.038	0.029	0.029	0.020	0.045	0.095	0.700	0.250	0.275	0.325	0.231
27	0.049	0.038	0.029	0.029	0.020	0.043	0.095	0.700	0.250	0.275	0.300	0.184
28	0.049	0.038	0.029	0.029	0.020	0.043	0.098	0.475	0.250	0.275	0.275	0.155
29	0.043	0.038	0.029	0.029	-----	0.042	0.184	0.450	0.250	0.300	0.275	0.142
30	0.043	0.038	0.029	0.029	-----	0.040	0.184	0.450	0.250	0.300	0.250	0.133
31	0.043	-----	0.029	0.029	-----	0.045	-----	0.450	-----	0.300	0.275	-----
Maks.	0.325	0.043	0.038	0.029	0.029	0.155	0.184	0.700	0.900	0.300	0.500	0.400
Min.	0.043	0.038	0.029	0.029	0.019	0.009	0.066	0.086	0.250	0.241	0.250	0.133
Ortalama	0.072	0.041	0.034	0.029	0.025	0.039	0.102	0.218	0.475	0.254	0.340	0.281
LT/SN/Km2	0.116	0.065	0.054	0.046	0.039	0.062	0.162	0.348	0.759	0.405	0.542	0.449
AKIM mm.	0.310	0.169	0.144	0.124	0.095	0.166	0.421	0.933	1.97	1.09	1.45	1.16
MİL. M3	0.194	0.106	0.090	0.078	0.059	0.104	0.263	0.584	1.23	0.680	0.909	0.728

SU YILI (2006) YILLIK TOPLAM AKIM 5.03 MİLYON M3 8 MM. 0.3 LT/SN/Km2

08. Bati Akdeniz Havzasi

D08A094 DEGİRMENDERE DEREKÖY

YERİ : **MİLAS-ÖREN KARAYOLU ÜZERİNDEKİ DEREKÖY KÖPRÜSÜNÜN,1KM MANSABINDADIR. 27°56'22" Doğu - 37°5'24" Kuzey**

YAĞIŞ ALANI : **51,00 km2** **YAKLAŞIK KOT : 135 m**

GÖZLEM SÜRESİ : **29.07.1984 - 30.09.2006**

ORTALAMA AKIMLAR : **Gözlem süresinde 0.185 m3/sn. (3 Yıllık) 2006 Su yılında 0.185 m3/sn.**

ANLIK EN ÇOK VE EN AZ AKIMLAR:

2006 Su yılında anlık ençok akım	**:**	**9.15**	**m3/sn**	**26.11.2005**
2006 Su yılında anlık enaz akım	**:**	**0.001**	**m3/sn**	**22.09.2006**
Gözlem süresinde anlık ençok akım	**:**	**9.15**	**m3/sn**	**26.11.2005**
Gözlem süresinde anlık enaz akım	**:**	**0.001**	**m3/sn**	**22.09.2006**

Akımlar 01 Ekim 2005 'den 30 Eylül 2006' a kadar m3/sn olarak

Gün	Ekim	Kasım	Aralık	Ocak	Şubat	Mart	Nisan	Mayıs	Haziran	Temmuz	Ağustos	Eylül
01	0.062	0.003	0.139	0.062	0.139	0.358	0.512	0.113	0.088	0.062	0.046	0.046
02	0.400	0.003	0.139	0.062	0.113	0.316	0.512	0.113	0.088	0.046	0.046	0.046
03	0.113	0.009	0.139	0.062	0.113	0.316	0.512	0.113	0.088	0.046	0.046	0.046
04	0.046	0.033	0.139	0.062	0.113	0.274	0.358	0.113	0.088	0.062	0.046	0.046
05	0.046	0.015	0.139	0.062	0.113	0.232	0.316	0.113	0.088	0.062	0.046	0.046
06	0.033	0.015	0.139	0.062	0.400	0.232	0.316	0.113	0.088	0.062	0.046	0.046
07	0.023	0.015	0.139	0.062	0.680	0.358	0.316	0.113	0.088	0.062	0.046	0.046
08	0.023	0.015	0.139	0.062	0.750	1.19	0.316	0.113	0.088	0.062	0.046	0.046
09	0.023	0.015	0.139	0.062	0.512	0.624	0.316	0.113	0.062	0.046	0.046	0.046
10	0.023	0.009	0.139	0.062	0.456	0.680	0.316	0.113	0.062	0.046	0.046	0.046
11	0.023	0.009	0.139	0.062	0.624	0.680	0.316	0.113	0.062	0.046	0.046	0.046
12	0.023	0.009	0.139	0.062	0.680	0.890	0.316	0.113	0.062	0.062	0.046	0.046
13	0.015	0.009	0.139	0.062	0.512	2.04	0.316	0.113	0.062	0.046	0.046	0.046
14	0.009	0.015	0.139	0.062	0.400	1.69	0.316	0.113	0.062	0.062	0.046	0.046
15	0.009	0.015	0.190	0.062	0.400	1.28	0.400	0.113	0.062	0.062	0.062	0.046
16	0.005	0.015	0.164	0.062	0.274	1.19	0.316	0.113	0.062	0.046	0.088	0.046
17	0.005	0.033	0.164	0.062	0.274	0.890	0.274	0.113	0.062	0.046	0.062	0.046
18	0.005	0.088	0.139	0.062	0.568	0.750	0.274	0.113	0.062	0.046	0.062	0.046
19	0.005	0.062	1.36	0.062	0.400	0.750	0.274	0.113	0.062	0.062	0.062	0.046
20	0.005	0.046	0.400	0.139	0.456	0.750	0.190	0.113	0.062	0.046	0.062	0.046
21	0.005	0.033	0.190	0.088	0.358	0.680	0.190	0.113	0.062	0.088	0.062	0.046
22	0.005	0.033	0.139	0.062	0.316	0.568	0.190	0.113	0.088	0.088	0.046	0.046
23	0.005	0.033	0.113	0.512	0.316	0.512	0.190	0.113	0.062	0.062	0.046	0.062
24	0.005	0.033	0.113	0.624	0.274	0.512	0.190	0.113	0.062	0.062	0.046	0.046
25	0.005	0.033	0.062	0.890	0.316	0.512	0.190	0.113	0.062	0.046	0.046	0.062
26	0.005	3.30	0.088	0.512	0.316	0.512	0.190	0.113	0.062	0.046	0.046	0.046
27	0.005	0.624	0.088	0.456	0.316	0.512	0.190	0.113	0.046	0.062	0.046	0.046
28	0.003	0.164	0.062	0.316	0.316	0.512	0.190	0.113	0.062	0.088	0.046	0.046
29	0.003	0.139	0.062	0.232	-----	0.512	0.139	0.113	0.062	0.062	0.046	0.046
30	0.003	0.139	0.062	0.164	-----	0.512	0.139	0.113	0.062	0.046	0.046	0.046
31	0.003	-----	0.062	0.139	-----	0.512	-----	0.113	-----	0.062	0.046	-----
Maks.	1.85	9.15	2.42	1.60	1.28	6.10	0.512	0.232	0.164	0.190	0.190	0.139
Min.	0.003	0.003	0.062	0.062	0.113	0.139	0.139	0.033	0.015	0.046	0.046	0.001
Ortalama	0.030	0.165	0.174	0.171	0.375	0.689	0.286	0.113	0.069	0.058	0.050	0.047
LT/SN/Km2	0.596	3.24	3.42	3.36	7.36	13.5	5.61	2.22	1.36	1.13	0.989	0.923
AKIM mm.	1.60	8.41	9.16	9.00	17.8	36.2	14.5	5.93	3.52	3.04	2.65	2.39
MİL. M3	0.081	0.429	0.467	0.459	0.908	1.84	0.741	0.303	0.180	0.155	0.135	0.122

SU YILI (2006) YILLIK TOPLAM AKIM 5.82 MİLYON M3 114 MM. 3.6 LT/SN/Km2

08. Bati Akdeniz Havzasi

D08A095 MİMİR D. YİLMAZLI

YERİ : **ELMALI İLÇESINDEN ESKI PAZAR KASABASI GÜĞÜ KÖYÜ ISTIKKAMETINDE GÜĞÜ VE DEREKÖY DERELERININ BIRLEYTIĞI NOKTAYA VARILIR.YILMAZLI KÖYÜ İSTIKAMETINDE 300. METREDEDIR. 29°48'27" Doğu - 36°48'0" Kuzey**

YAĞIŞ ALANI : **196,16 km2** **YAKLAŞIK KOT : 1070 m**

GÖZLEM SÜRESİ : **01.10.1984 - 30.09.2006**

ORTALAMA AKIMLAR : **Gözlem süresinde 0.573 m3/sn. (21 Yıllık) 2006 Su yılında 0.384 m3/sn.**

ANLIK EN ÇOK VE EN AZ AKIMLAR:

2006 Su yılında anlık ençok akım	:	**16.5**	**m3/sn**	**15.04.2006**
2006 Su yılında anlık enaz akım	:	**0.000**	**m3/sn**	**01.10.2005**
Gözlem süresinde anlık ençok akım	:	**103.**	**m3/sn**	**28.07.1989**
Gözlem süresinde anlık enaz akım	:	**0.000**	**m3/sn**	**01.08.1986**

Akımlar 01 Ekim 2005 'den 30 Eylül 2006' a kadar m3/sn olarak

Gün	Ekim	Kasım	Aralık	Ocak	Şubat	Mart	Nisan	Mayıs	Haziran	Temmuz	Ağustos	Eylül
01	KURU	KURU	KURU	KURU	KURU	0.013	2.85	1.40	0.010	0.078	KURU	KURU
02	KURU	KURU	KURU	KURU	KURU	0.023	2.85	1.30	0.004	0.061	KURU	KURU
03	KURU	KURU	KURU	KURU	KURU	0.044	2.85	1.20	0.006	0.044	KURU	KURU
04	KURU	KURU	KURU	KURU	KURU	0.104	2.85	1.10	0.006	0.078	KURU	KURU
05	KURU	KURU	KURU	KURU	KURU	0.130	2.70	1.10	0.006	0.078	KURU	KURU
06	KURU	KURU	KURU	KURU	KURU	0.130	2.55	0.980	0.010	0.130	KURU	KURU
07	KURU	KURU	KURU	KURU	KURU	0.200	2.70	0.860	0.010	0.078	KURU	KURU
08	KURU	KURU	KURU	KURU	KURU	0.200	2.85	0.770	0.010	0.061	KURU	KURU
09	KURU	KURU	KURU	KURU	KURU	0.165	2.70	0.680	0.010	0.034	KURU	KURU
10	KURU	KURU	KURU	KURU	KURU	0.104	2.55	0.600	0.010	0.023	KURU	KURU
11	KURU	KURU	KURU	KURU	KURU	0.078	2.70	0.520	0.010	0.023	KURU	KURU
12	KURU	KURU	KURU	KURU	KURU	0.078	2.70	0.520	0.010	0.018	KURU	KURU
13	KURU	KURU	KURU	KURU	KURU	0.165	2.70	0.460	0.010	0.018	KURU	KURU
14	KURU	KURU	KURU	KURU	KURU	0.345	2.70	0.400	0.010	0.013	KURU	KURU
15	KURU	KURU	KURU	KURU	KURU	0.400	6.24	0.345	0.010	0.010	KURU	KURU
16	KURU	KURU	KURU	KURU	KURU	0.520	6.24	0.400	0.010	0.006	KURU	KURU
17	KURU	KURU	KURU	KURU	KURU	0.600	4.76	0.520	0.010	KURU	KURU	KURU
18	KURU	KURU	KURU	KURU	KURU	0.770	4.10	0.400	0.010	KURU	KURU	KURU
19	KURU	KURU	KURU	KURU	KURU	0.980	3.44	0.345	0.010	KURU	KURU	KURU
20	KURU	KURU	KURU	KURU	KURU	1.20	3.00	0.290	0.010	KURU	KURU	KURU
21	KURU	KURU	KURU	KURU	KURU	1.60	2.70	0.290	0.010	KURU	KURU	KURU
22	KURU	KURU	KURU	KURU	KURU	2.00	2.55	0.245	0.010	KURU	KURU	KURU
23	KURU	KURU	KURU	KURU	KURU	2.55	2.85	0.165	0.010	KURU	KURU	KURU
24	KURU	KURU	KURU	KURU	KURU	2.70	2.70	0.130	0.010	KURU	KURU	KURU
25	KURU	KURU	KURU	KURU	0.004	2.70	2.20	0.104	0.010	KURU	KURU	KURU
26	KURU	KURU	KURU	KURU	0.023	2.55	1.85	0.078	0.013	KURU	KURU	KURU
27	KURU	KURU	KURU	KURU	0.013	2.70	1.70	0.061	0.130	KURU	KURU	KURU
28	KURU	KURU	KURU	KURU	0.006	3.00	1.70	0.044	0.860	KURU	KURU	KURU
29	KURU	KURU	KURU	KURU	-----	2.85	1.60	0.034	0.165	KURU	KURU	KURU
30	KURU	KURU	KURU	KURU	-----	3.22	1.50	0.023	0.104	KURU	KURU	KURU
31	KURU	-----	KURU	KURU	-----	3.00	-----	0.023	-----	KURU	KURU	-----
Maks.	KURU	KURU	KURU	KURU	0.023	4.32	16.5	1.40	5.20	0.290	KURU	KURU
Min.	KURU	KURU	KURU	KURU	KURU	KURU	1.40	0.023	0.004	KURU	KURU	KURU
Ortalama	KURU	KURU	KURU	KURU	0.002	1.13	2.91	0.496	0.050	0.024	KURU	KURU
LT/SN/Km2	0.000	0.000	0.000	0.000	0.008	5.78	14.8	2.53	0.256	0.124	0.000	0.000
AKIM mm.	0.000	0.000	0.000	0.000	0.020	15.5	38.5	6.78	0.662	0.332	0.000	0.000
MİL. M3	0.000	0.000	0.000	0.000	0.004	3.03	7.55	1.33	0.130	0.065	0.000	0.000

SU YILI (2006) YILLIK TOPLAM AKIM 12.11 MİLYON M3 62 MM. 2.0 LT/SN/Km2

08. Bati Akdeniz Havzasi

D08A096 DEĞİRMEN D. MİLAS

YERİ : **MİLAS'A 2KM MESAFEDE MİLAS-YUSUFÇA YOLUNDAKI KIRKAHVELER MEVKİİ HAYIR SEVENLER KÖPRÜSÜNDEDIR**

27°48'41" Doğu - 37°19'15" Kuzey

YAĞIŞ ALANI : **49,50 km2** **YAKLAŞIK KOT : 50 m**

GÖZLEM SÜRESİ : **01.07.1985 - 30.09.2006**

ORTALAMA AKIMLAR : **Gözlem süresinde 0.161 m3/sn. (11 Yıllık) 2006 Su yılında 0.161 m3/sn.**

ANLIK EN ÇOK VE EN AZ AKIMLAR:

2006 Su yılında anlık ençok akım	**:**	**13.1**	**m3/sn**	**14.03.2006**
2006 Su yılında anlık enaz akım	**:**	**0.000**	**m3/sn**	**21.10.2005**
Gözlem süresinde anlık ençok akım	**:**	**14.3**	**m3/sn**	**29.03.1999**
Gözlem süresinde anlık enaz akım	**:**	**0.000**	**m3/sn**	**01.10.1986**

Akımlar 01 Ekim 2005 'den 30 Eylül 2006' a kadar m3/sn olarak

Gün	Ekim	Kasım	Aralık	Ocak	Şubat	Mart	Nisan	Mayıs	Haziran	Temmuz	Ağustos	Eylül
01	KURU	KURU	0.006	0.039	0.068	0.271	0.184	0.068	0.001	0.003	0.056	0.012
02	0.740	0.001	0.006	0.008	0.039	0.184	0.184	0.155	0.097	0.001	0.068	0.016
03	0.380	0.002	0.005	0.008	0.010	0.155	0.155	0.271	0.097	0.005	0.056	0.002
04	0.200	0.008	0.003	0.006	0.010	0.155	0.155	0.184	0.068	0.003	0.044	0.002
05	0.128	0.005	0.005	0.068	0.010	0.126	0.155	0.213	0.008	0.001	0.032	0.002
06	0.152	0.002	0.003	0.097	0.600	0.126	0.155	0.184	0.010	0.001	0.032	0.002
07	0.008	0.002	0.001	0.068	3.24	0.184	0.155	0.213	0.008	0.097	0.016	0.002
08	KURU	0.002	0.001	0.068	0.900	0.600	0.155	0.184	0.006	0.003	0.012	0.002
09	KURU	0.002	0.001	0.039	0.300	1.10	0.126	0.184	0.001	0.006	0.008	0.002
10	KURU	0.002	0.001	0.039	0.400	0.300	0.126	0.126	0.003	0.242	0.005	0.002
11	KURU	0.002	0.001	0.039	2.40	0.242	0.126	0.155	0.005	0.213	0.005	0.001
12	KURU	0.001	0.001	0.039	3.24	0.213	0.097	0.155	0.005	0.010	0.005	0.001
13	KURU	0.002	0.001	0.039	0.900	2.54	0.097	0.242	0.126	0.003	0.005	0.001
14	KURU	0.002	0.001	0.010	0.400	4.48	0.184	0.184	0.155	0.006	0.005	0.001
15	KURU	0.002	0.184	0.010	0.271	1.20	0.213	0.039	0.006	0.008	0.005	0.001
16	KURU	0.032	0.006	0.039	0.242	0.700	0.155	0.039	0.001	0.097	0.005	0.001
17	KURU	0.104	0.005	0.039	0.213	0.500	0.155	0.097	0.001	0.008	0.005	0.001
18	KURU	1.43	0.006	0.039	0.213	0.400	0.126	0.068	0.001	0.006	0.005	0.001
19	KURU	0.560	1.63	0.068	0.184	0.400	0.126	0.010	0.001	0.010	0.005	0.001
20	KURU	0.680	0.242	0.097	0.184	0.300	0.155	0.008	0.001	0.006	0.005	0.001
21	KURU	0.500	0.126	0.039	0.155	0.300	0.126	0.097	0.001	0.001	0.005	0.001
22	KURU	0.380	0.097	0.039	0.155	0.271	0.097	0.006	0.001	0.001	0.005	0.001
23	KURU	0.380	0.097	0.097	0.155	0.242	0.068	0.008	0.001	0.001	0.005	0.008
24	KURU	0.320	0.068	0.155	0.155	0.271	0.068	0.006	0.008	0.010	0.005	0.032
25	KURU	0.320	0.068	1.41	0.155	0.271	0.068	0.005	0.005	0.200	0.005	0.128
26	KURU	2.68	0.039	0.213	0.155	0.242	0.068	0.006	0.006	0.128	0.005	0.104
27	KURU	0.184	0.039	0.126	0.155	0.213	0.039	0.001	0.003	0.068	0.005	0.440
28	KURU	0.039	0.006	0.126	0.155	0.213	0.006	0.001	0.039	0.176	0.005	0.380
29	KURU	0.008	0.006	0.097	-----	0.213	0.097	0.003	0.300	0.056	0.005	0.380
30	KURU	0.006	0.008	0.097	-----	0.184	0.068	0.001	0.213	0.080	0.005	0.380
31	KURU	-----	0.010	0.068	-----	0.184	-----	0.001	-----	0.056	0.008	-----
Maks.	7.97	7.10	5.50	3.52	10.0	13.1	0.271	0.600	0.600	0.600	0.500	6.48
Min.	KURU	KURU	0.001	0.003	0.008	0.126	KURU	KURU	KURU	KURU	0.005	KURU
Ortalama	0.052	0.255	0.086	0.107	0.538	0.541	0.123	0.094	0.039	0.049	0.014	0.064
LT/SN/Km2	1.05	5.16	1.74	2.17	10.9	10.9	2.48	1.90	0.793	0.981	0.285	1.28
AKIM mm.	2.81	13.4	4.67	5.81	26.3	29.3	6.44	5.09	2.06	2.63	0.763	3.33
MİL. M3	0.139	0.662	0.231	0.287	1.30	1.45	0.319	0.252	0.102	0.130	0.038	0.165

SU YILI (2006) YILLIK TOPLAM AKIM 5.08 MİLYON M3 103 MM. 3.3 LT/SN/Km2

08. Bati Akdeniz Havzasi

D08A099 KANDAK Ç. SELİMİYE

YERİ : **MİLAS-SELİMİYE'DEN KANDAK'A AYRILAN YOLUN 2.KM.SİNDEDİR. .**
27°39'12" Doğu - 37°25'14" Kuzey

YAĞIŞ ALANI : **28,30 km2** **YAKLAŞIK KOT : 59 m**

GÖZLEM SÜRESİ : **31.01.1986 - 30.09.2006**

ORTALAMA AKIMLAR : **Gözlem süresinde 0.318 m3/sn. (10 Yıllık) 2006 Su yılında 0.308 m3/sn.**

ANLIK EN ÇOK VE EN AZ AKIMLAR:

2006 Su yılında anlık ençok akım	**:**	**25.0**	**m3/sn**	**26.11.2005**
2006 Su yılında anlık enaz akım	**:**	**0.000**	**m3/sn**	**01.10.2005**
Gözlem süresinde anlık ençok akım	**:**	**67.6**	**m3/sn**	**17.12.2001**
Gözlem süresinde anlık enaz akım	**:**	**0.000**	**m3/sn**	**01.10.1986**

Akımlar 01 Ekim 2005 'den 30 Eylül 2006' a kadar m3/sn olarak

Gün	Ekim	Kasım	Aralık	Ocak	Şubat	Mart	Nisan	Mayıs	Haziran	Temmuz	Ağustos	Eylül
01	KURU	KURU	0.070	1.90	0.114	0.202	0.290	0.070	0.015	0.003	KURU	KURU
02	KURU	KURU	0.070	1.25	0.114	0.202	0.246	0.070	0.015	0.003	KURU	KURU
03	KURU	KURU	0.070	1.25	0.114	0.202	0.202	0.070	0.015	0.003	KURU	KURU
04	KURU	KURU	0.070	1.25	0.114	0.202	0.202	0.070	0.015	0.003	KURU	KURU
05	KURU	KURU	0.070	3.05	0.114	0.158	0.246	0.070	0.015	0.003	KURU	KURU
06	KURU	KURU	0.070	2.18	0.920	0.158	0.246	0.070	0.015	0.003	KURU	KURU
07	KURU	KURU	0.070	3.70	1.14	0.158	0.202	0.070	0.015	0.003	KURU	KURU
08	KURU	KURU	0.070	0.290	0.920	4.23	0.158	0.070	0.015	0.003	KURU	KURU
09	KURU	KURU	0.070	0.158	0.536	1.25	0.158	0.070	0.015	0.003	KURU	KURU
10	KURU	KURU	0.070	0.158	0.810	0.920	0.158	0.070	0.015	0.003	KURU	KURU
11	KURU	KURU	0.070	0.158	1.38	0.810	0.158	0.070	0.015	0.001	KURU	KURU
12	KURU	KURU	0.042	0.114	1.25	0.700	0.158	0.070	0.015	KURU	KURU	KURU
13	KURU	KURU	0.042	0.114	0.700	10.4	0.158	0.070	0.007	KURU	KURU	KURU
14	KURU	KURU	0.070	0.114	0.536	4.05	0.158	0.070	0.007	KURU	KURU	KURU
15	KURU	KURU	0.290	0.114	0.454	0.700	0.158	0.070	0.007	KURU	KURU	KURU
16	KURU	KURU	0.246	0.070	0.372	0.536	0.114	0.070	0.007	KURU	KURU	KURU
17	KURU	KURU	0.246	0.070	0.372	0.372	0.114	0.070	0.007	KURU	KURU	KURU
18	KURU	4.05	0.290	0.070	0.454	0.372	0.114	0.070	0.007	KURU	KURU	KURU
19	KURU	4.40	0.454	0.114	0.454	0.372	0.114	0.070	0.007	KURU	KURU	KURU
20	KURU	0.290	0.372	0.158	0.372	0.372	0.114	0.070	0.007	KURU	KURU	KURU
21	KURU	0.290	0.290	0.158	0.372	0.372	0.114	0.070	0.007	KURU	KURU	KURU
22	KURU	0.290	0.246	0.158	0.372	0.372	0.114	0.070	0.007	KURU	KURU	KURU
23	KURU	0.290	0.246	0.158	0.372	0.372	0.114	0.070	0.003	KURU	KURU	KURU
24	KURU	0.290	0.246	0.202	0.372	0.372	0.114	0.070	0.003	KURU	KURU	KURU
25	KURU	0.454	0.202	0.202	0.290	0.372	0.070	0.070	0.003	KURU	KURU	KURU
26	KURU	23.5	0.202	0.202	0.290	0.372	0.070	0.070	0.003	KURU	KURU	KURU
27	KURU	3.35	0.202	0.202	0.290	0.290	0.070	0.070	0.003	KURU	KURU	KURU
28	KURU	0.290	0.202	0.158	0.202	0.290	0.070	0.070	0.003	KURU	KURU	KURU
29	KURU	0.158	0.202	0.158	-----	0.290	0.070	0.026	0.003	KURU	KURU	KURU
30	KURU	0.114	0.202	0.114	-----	0.290	0.070	0.015	0.003	KURU	KURU	KURU
31	KURU	-----	1.03	0.114	-----	0.290	-----	0.015	-----	KURU	KURU	-----
Maks.	0.001	25.0	16.0	9.47	3.53	17.5	0.536	0.158	0.246	0.042	KURU	KURU
Min.	KURU	KURU	0.042	0.070	0.007	0.158	0.070	0.015	0.001	KURU	KURU	KURU
Ortalama	KURU	1.26	0.197	0.584	0.493	0.969	0.145	0.065	0.009	0.001	KURU	KURU
LT/SN/Km2	0.000	44.5	6.94	20.6	17.4	34.3	5.12	2.30	0.323	0.035	0.000	0.000
AKIM mm.	0.000	115.	18.6	55.3	42.1	91.7	13.3	6.15	0.837	0.095	0.000	0.000
MİL. M3	0.000	3.26	0.526	1.56	1.19	2.60	0.375	0.174	0.024	0.003	0.000	0.000

SU YILI (2006) YILLIK TOPLAM AKIM 9.71 MİLYON M3 343 MM. 10.9 LT/SN/Km2

08. Bati Akdeniz Havzasi

D08A100 KARABALÇIK D. ÇOBANİSA

YERİ : **FETHİYE-KORKUTELİ YOLUNUN 78.KM.SİNDEN ŞOLA AYRILAN YOLDAN 4KM.GİDİLEREK İSTASYONA ULAŞILIR.İSTASYON ÇAMYAKASI TEPESİ MEVKİİNDEDİR..**
29°40'24" Doğu - 36°57'21" Kuzey

YAĞIŞ ALANI : **21,00 km2** **YAKLAŞIK KOT : 1280 m**

GÖZLEM SÜRESİ : **22.09.1987 - 30.09.2006**

ORTALAMA AKIMLAR : **Gözlem süresinde 0.149 m3/sn. (18 Yıllık) 2006 Su yılında 0.126 m3/sn.**

ANLIK EN ÇOK VE EN AZ AKIMLAR:

2006 Su yılında anlık ençok akım	:	**2.39**	**m3/sn**	**23.04.2006**
2006 Su yılında anlık enaz akım	:	**0.000**	**m3/sn**	**01.10.2005**
Gözlem süresinde anlık ençok akım	:	**18.4**	**m3/sn**	**25.12.2002**
Gözlem süresinde anlık enaz akım	:	**0.000**	**m3/sn**	**01.10.1987**

Akımlar 01 Ekim 2005 'den 30 Eylül 2006' a kadar m3/sn olarak

Gün	Ekim	Kasım	Aralık	Ocak	Şubat	Mart	Nisan	Mayıs	Haziran	Temmuz	Ağustos	Eylül
01	KURU	0.004	0.013	0.027	0.133	0.435	0.594	0.207	0.027	0.013	0.013	KURU
02	KURU	0.004	0.013	0.027	0.133	0.435	0.594	0.207	0.027	0.013	0.013	KURU
03	KURU	0.004	0.013	0.027	0.133	0.541	0.541	0.207	0.027	0.013	0.013	KURU
04	KURU	0.004	0.013	0.027	0.133	0.435	0.541	0.207	0.027	0.013	0.013	KURU
05	KURU	0.004	0.013	0.027	0.133	0.389	0.488	0.180	0.027	0.027	0.013	KURU
06	KURU	0.004	0.013	0.027	0.133	0.389	0.435	0.180	0.027	0.027	0.013	KURU
07	0.004	0.013	0.013	0.027	0.133	0.389	0.435	0.180	0.027	0.027	KURU	KURU
08	0.004	0.013	0.013	0.027	0.133	0.389	0.435	0.180	0.027	0.027	KURU	KURU
09	0.004	0.013	0.013	0.027	0.133	0.298	0.389	0.180	0.027	0.013	KURU	KURU
10	0.004	0.013	0.013	0.027	0.133	0.253	0.344	0.180	0.027	0.013	KURU	KURU
11	0.004	0.013	0.013	0.027	0.700	0.253	0.344	0.102	0.013	0.013	KURU	KURU
12	0.004	0.013	0.013	0.013	0.488	0.298	0.298	0.102	0.013	0.013	KURU	KURU
13	0.004	0.013	0.013	0.027	0.344	0.344	0.298	0.102	0.013	0.013	KURU	KURU
14	0.004	0.013	0.013	0.027	0.207	0.298	0.298	0.102	0.013	0.013	KURU	KURU
15	0.004	0.013	0.013	0.013	0.180	0.435	0.647	0.102	0.013	0.013	KURU	KURU
16	0.004	0.013	0.027	0.013	0.133	0.541	0.488	0.072	0.013	0.013	KURU	KURU
17	0.004	0.013	0.027	0.027	0.180	0.700	0.344	0.072	0.013	0.013	KURU	KURU
18	0.004	0.072	0.027	0.027	0.180	0.700	0.344	0.072	0.013	0.013	KURU	KURU
19	0.004	0.133	0.048	0.027	0.207	0.772	0.298	0.072	0.013	0.013	KURU	KURU
20	0.004	0.389	0.072	0.072	0.207	0.916	0.253	0.048	0.013	0.013	KURU	KURU
21	0.004	0.344	0.072	0.072	0.344	0.916	0.253	0.048	0.004	0.013	KURU	KURU
22	0.004	0.298	0.048	0.072	0.344	0.772	0.253	0.048	0.004	0.013	KURU	KURU
23	0.004	0.253	0.048	0.072	0.389	0.916	0.594	0.048	0.004	0.013	KURU	KURU
24	0.004	0.207	0.048	0.102	0.488	0.844	0.435	0.048	0.004	0.013	KURU	KURU
25	0.004	0.180	0.048	0.133	0.488	0.844	0.344	0.048	0.004	0.013	KURU	KURU
26	0.004	0.133	0.048	0.133	0.435	0.700	0.298	0.048	0.004	0.013	KURU	KURU
27	0.004	0.102	0.027	0.133	0.435	0.700	0.253	0.048	0.013	0.013	KURU	KURU
28	0.004	0.072	0.027	0.133	0.389	0.700	0.253	0.048	0.013	0.013	KURU	KURU
29	0.004	0.048	0.027	0.133	-----	0.647	0.298	0.048	0.013	0.013	KURU	KURU
30	0.004	0.013	0.027	0.133	-----	0.647	0.253	0.048	0.013	0.013	KURU	KURU
31	0.004	-----	0.027	0.133	-----	0.700	-----	0.048	-----	0.013	KURU	-----
Maks.	0.004	0.389	0.435	0.207	1.15	1.90	2.39	0.207	0.298	0.647	0.013	KURU
Min.	KURU	0.004	KURU	0.013	0.004	0.207	0.253	0.004	KURU	0.013	KURU	KURU
Ortalama	0.003	0.080	0.027	0.058	0.267	0.568	0.388	0.106	0.016	0.015	0.003	KURU
LT/SN/Km2	0.154	3.83	1.29	2.75	12.7	27.0	18.5	5.04	0.756	0.705	0.120	0.000
AKIM mm.	0.411	9.92	3.47	7.37	30.7	72.4	47.9	13.5	1.96	1.89	0.321	0.000
MİL. M3	0.009	0.208	0.073	0.155	0.645	1.52	1.01	0.284	0.041	0.040	0.007	0.000

SU YILI (2006) YILLIK TOPLAM AKIM 3.99 MİLYON M3 190 MM. 6.0 LT/SN/Km2

08. Bati Akdeniz Havzasi

D08A101 KOCAÇAY EPÇE

YERİ : **MİLAS-EPÇE YOLU ÜZERİNDEKİ AT AHIRI MEVKİİNDEDİR.**
27°45'40" Doğu - 37°23'20" Kuzey

YAĞIŞ ALANI : **70,90 km2** **YAKLAŞIK KOT : 25 m**

GÖZLEM SÜRESİ : **30.01.1986 - 30.09.2006**

ORTALAMA AKIMLAR : **Gözlem süresinde 0.491 m3/sn. (8 Yıllık) 2006 Su yılında 0.491 m3/sn.**

ANLIK EN ÇOK VE EN AZ AKIMLAR:

2006 Su yılında anlık ençok akım	**:**	**57.0**	**m3/sn**	**26.11.2005**
2006 Su yılında anlık enaz akım	**:**	**0.000**	**m3/sn**	**01.10.2005**
Gözlem süresinde anlık ençok akım	**:**	**74.5**	**m3/sn**	**17.03.2000**
Gözlem süresinde anlık enaz akım	**:**	**0.000**	**m3/sn**	**01.10.1993**

Akımlar 01 Ekim 2005 'den 30 Eylül 2006' a kadar m3/sn olarak

Gün	Ekim	Kasım	Aralık	Ocak	Şubat	Mart	Nisan	Mayıs	Haziran	Temmuz	Ağustos	Eylül
01	KURU	KURU	0.004	0.443	0.443	1.75	0.217	0.145	0.007	KURU	KURU	KURU
02	0.004	KURU	0.004	0.348	0.443	0.806	0.217	0.109	0.006	KURU	KURU	KURU
03	KURU	KURU	0.004	0.348	0.443	0.648	0.217	0.109	0.003	KURU	KURU	KURU
04	KURU	KURU	0.004	0.348	0.395	0.648	0.217	0.109	0.003	KURU	KURU	KURU
05	KURU	KURU	0.004	2.07	0.395	0.648	0.217	0.109	0.003	KURU	KURU	KURU
06	KURU	KURU	0.004	0.885	5.20	0.648	0.217	0.109	0.002	KURU	KURU	KURU
07	KURU	KURU	0.004	3.03	7.00	3.03	0.217	0.109	0.002	KURU	KURU	KURU
08	KURU	KURU	0.004	0.443	3.42	11.6	0.217	0.109	0.002	KURU	KURU	KURU
09	KURU	KURU	0.004	0.300	1.32	3.23	0.217	0.073	0.001	KURU	KURU	KURU
10	KURU	KURU	0.004	0.300	7.30	0.885	0.217	0.059	0.001	KURU	KURU	KURU
11	KURU	KURU	0.004	0.300	20.7	0.727	0.217	0.059	0.001	KURU	KURU	KURU
12	KURU	KURU	0.003	0.253	6.20	0.648	0.217	0.059	0.001	KURU	KURU	KURU
13	KURU	KURU	0.003	0.253	1.91	11.6	0.217	0.059	KURU	KURU	KURU	KURU
14	KURU	KURU	0.004	0.253	1.10	7.90	0.217	0.059	KURU	KURU	KURU	KURU
15	KURU	KURU	0.443	0.253	0.994	0.885	0.217	0.059	KURU	KURU	KURU	KURU
16	KURU	KURU	0.300	0.253	0.727	0.443	0.217	0.059	KURU	KURU	KURU	KURU
17	KURU	KURU	0.300	0.253	1.21	0.300	0.217	0.047	KURU	KURU	KURU	KURU
18	KURU	0.181	0.490	0.253	4.41	0.300	0.217	0.047	KURU	KURU	KURU	KURU
19	KURU	0.003	3.42	5.60	1.21	0.300	0.253	0.047	KURU	KURU	KURU	KURU
20	KURU	0.020	0.395	3.03	0.885	0.253	0.253	0.047	KURU	KURU	KURU	KURU
21	KURU	0.001	0.348	0.806	0.727	0.253	0.253	0.047	KURU	KURU	KURU	KURU
22	KURU	KURU	0.348	0.806	0.727	0.253	0.217	0.047	KURU	KURU	KURU	KURU
23	KURU	KURU	0.348	0.806	0.727	0.253	0.253	0.047	KURU	KURU	KURU	KURU
24	KURU	KURU	0.348	2.55	0.727	0.253	0.181	0.047	KURU	KURU	KURU	0.002
25	KURU	KURU	0.348	5.40	0.727	0.253	0.181	0.038	KURU	KURU	KURU	0.001
26	KURU	5.80	0.348	1.10	0.727	0.253	0.181	0.038	KURU	KURU	KURU	KURU
27	KURU	0.028	0.348	0.648	0.727	0.253	0.181	0.038	KURU	KURU	KURU	KURU
28	KURU	0.016	0.348	0.569	0.648	0.253	0.145	0.020	KURU	KURU	KURU	KURU
29	KURU	0.007	0.348	0.490	-----	0.217	0.145	0.011	KURU	KURU	KURU	KURU
30	KURU	0.006	0.348	0.443	-----	0.217	0.145	0.011	KURU	KURU	KURU	KURU
31	KURU	-----	1.32	0.443	-----	0.217	-----	0.011	-----	KURU	KURU	-----
Maks.	7.90	57.0	17.2	30.6	38.5	45.5	24.8	0.145	0.020	KURU	KURU	3.82
Min.	KURU	KURU	0.003	0.059	0.395	0.217	0.001	0.011	KURU	KURU	KURU	KURU
Ortalama	0.000	0.202	0.329	1.07	2.55	1.61	0.210	0.062	0.001	KURU	KURU	0.000
LT/SN/Km2	0.002	2.85	4.64	15.1	36.0	22.7	2.96	0.881	0.015	0.000	0.000	0.001
AKIM mm.	0.005	7.39	12.4	40.6	87.1	60.8	7.67	2.36	0.039	0.000	0.000	0.004
MİL. M3	0.000	0.524	0.881	2.88	6.17	4.31	0.544	0.167	0.003	0.000	0.000	0.000

SU YILI (2006) YILLIK TOPLAM AKIM 15.48 MİLYON M3 218 MM. 6.9 LT/SN/Km2

08. Bati Akdeniz Havzasi

D08A103 DALAMAN Ç. ÇAMKÖY

YERİ : ISPARTA BURDUR-GÖLHİSAR YOLUNDAN YUSUFCA KASABASI YOLU İLE ÇAMKÖY'E 1 KM KALA DALAMAN ÇAYI KÖPRÜSÜNÜN SAĞ SAHİLİNDEDİR.
29°31'0" Doğu - 37°15'0" Kuzey

YAĞIŞ ALANI : 1752,00 km2 **YAKLAŞIK KOT :** 906 m

GÖZLEM SÜRESİ : 01.06.1986 - 30.09.2006

ORTALAMA AKIMLAR : Gözlem süresinde 4.018 m3/sn. (18 Yıllık) 2006 Su yılında 1.801 m3/sn.

ANLIK EN ÇOK VE EN AZ AKIMLAR:

2006 Su yılında anlık ençok akım	:	14.8	m3/sn	28.06.2006
2006 Su yılında anlık enaz akım	:	0.145	m3/sn	26.11.2005
Gözlem süresinde anlık ençok akım	:	78.0	m3/sn	25.04.2000
Gözlem süresinde anlık enaz akım	:	0.000	m3/sn	09.08.1987

2. Anahtar Eğrisi (Seviyeler cm olarak)

Seviye	Akım	Seviye	Akım	Seviye	Akım	Seviye	Akım
11	0.002	33	0.219	77	4.6	160	32.4
21	0.032	36	0.335	80	5.4	190	47.5
24	0.054	39	0.450	86	6.7	250	80.0
27	0.093	60	2.0	100	10.0	260	88.0
30	0.145	72	3.9	130	19.6	270	90.0

Akımlar 01 Ekim 2005 'den 30 Eylül 2006' a kadar m3/sn olarak

Gün	Ekim	Kasım	Aralık	Ocak	Şubat	Mart	Nisan	Mayıs	Haziran	Temmuz	Ağustos	Eylül
01	1.84	2.57	1.87	2.05	2.44	2.70	3.73	0.335	0.335	5.37	0.455	0.561
02	4.63	2.57	1.87	2.05	2.31	2.70	3.73	0.370	0.335	3.95	0.455	0.561
03	5.56	2.57	1.87	2.05	2.18	2.70	3.35	0.370	0.295	2.54	0.614	0.561
04	1.21	3.09	1.78	1.33	2.18	2.83	3.73	0.450	0.295	2.54	0.614	0.561
05	0.561	2.70	1.78	1.33	2.44	2.70	3.73	0.410	0.295	2.40	0.455	0.561
06	0.349	2.57	1.78	1.60	2.96	2.83	3.90	0.410	0.295	1.98	0.402	0.561
07	0.296	2.57	1.78	1.60	2.83	2.83	3.73	0.410	0.295	1.98	0.402	0.614
08	0.296	2.57	1.78	2.18	2.96	3.09	3.73	0.410	0.295	2.54	0.402	0.614
09	9.56	2.44	1.78	2.05	2.96	2.96	3.73	0.410	0.450	2.26	0.402	0.614
10	1.41	2.44	1.78	2.05	2.96	2.83	3.73	0.410	0.295	1.70	0.402	0.614
11	2.54	2.57	1.78	2.05	3.22	2.96	3.35	0.410	0.335	1.11	0.349	0.614
12	2.82	2.57	1.69	2.05	3.22	3.09	3.22	0.410	0.500	1.01	0.349	0.561
13	1.98	2.44	1.69	2.05	2.96	9.25	3.09	0.410	0.710	0.402	0.349	0.561
14	2.40	2.44	1.69	2.05	2.96	9.75	1.33	0.410	1.08	0.455	0.402	0.561
15	2.54	1.08	1.69	2.05	2.83	6.70	0.335	0.410	1.15	0.916	0.402	0.561
16	2.68	0.243	1.69	2.05	2.70	5.40	0.335	0.410	0.820	1.41	0.402	0.561
17	2.82	0.765	1.78	1.96	2.70	4.80	0.335	0.410	0.450	0.614	0.402	0.561
18	2.68	2.05	1.78	1.33	2.70	4.60	0.335	0.410	0.450	0.614	0.402	0.561
19	1.84	4.05	1.69	1.51	2.70	4.20	0.335	0.410	0.500	0.614	0.402	0.561
20	1.31	5.80	1.69	1.51	2.70	4.05	0.335	0.410	0.145	0.508	0.402	0.561
21	1.60	3.22	2.05	1.87	2.70	4.05	0.335	0.410	0.243	0.508	0.455	0.561
22	0.720	3.09	2.44	1.78	2.70	4.05	0.335	0.410	0.145	0.508	0.455	2.68
23	0.455	2.83	2.18	1.78	2.57	4.05	0.335	0.410	0.145	0.508	0.455	5.56
24	0.349	2.83	2.18	2.05	2.57	4.05	0.335	0.410	0.145	0.455	0.455	6.13
25	0.349	2.70	2.18	2.31	2.57	4.05	0.335	0.410	0.145	0.455	0.508	4.29
26	0.349	0.145	2.18	2.83	2.83	3.90	0.335	0.410	0.145	0.455	0.508	2.82
27	0.402	1.96	2.05	2.83	2.70	4.20	0.335	0.410	1.42	0.455	0.508	2.96
28	0.402	1.96	2.05	2.83	2.57	3.90	0.335	0.410	14.8	0.455	0.508	3.44
29	0.402	1.87	2.05	2.57	-----	3.73	0.335	0.370	5.75	0.455	0.508	3.44
30	0.349	1.87	2.05	2.44	-----	3.90	0.335	0.370	4.99	0.455	0.508	3.10
31	2.31	-----	2.05	2.44	-----	3.90	-----	0.335	-----	0.455	0.561	-----
Maks.	9.56	5.80	2.44	2.83	3.22	9.75	3.90	0.450	14.8	5.37	0.614	6.13
Min.	0.296	0.145	1.69	1.33	2.18	2.70	0.335	0.335	0.145	0.402	0.349	0.561
Ortalama	1.84	2.42	1.89	2.02	2.72	4.09	1.78	0.401	1.24	1.29	0.448	1.55
LT/SN/Km2	1.05	1.38	1.08	1.15	1.55	2.33	1.02	0.229	0.709	0.738	0.256	0.884
AKIM mm.	2.81	3.58	2.89	3.09	3.75	6.25	2.64	0.613	1.84	1.98	0.685	2.29
MİL. M3	4.93	6.27	5.07	5.41	6.58	11.0	4.62	1.07	3.22	3.46	1.20	4.01

SU YILI (2006) YILLIK TOPLAM AKIM 56.84 MİLYON M3 32 MM. 1.0 LT/SN/Km2

08. Bati Akdeniz Havzasi

D08A104 DEĞİRMENDERE AKALAN

YERİ : **ACIPAYAM-KELEKCİ YOLUNUN 7.KM.DEKİ AKALAN KASABASINDAN SAĞA AYRILAN YOLUN 2 KM.DEDİR**
29°21'0" Doğu - 37°23'0" Kuzey

YAĞIŞ ALANI : **34,50 km2** **YAKLAŞIK KOT : 1100 m**

GÖZLEM SÜRESİ : **01.02.1986 - 30.09.2006**

ORTALAMA AKIMLAR : **Gözlem süresinde 0.190 m3/sn. (16 Yıllık) 2006 Su yılında 0.144 m3/sn.**

ANLIK EN ÇOK VE EN AZ AKIMLAR:

2006 Su yılında anlık ençok akım	**:**	**3.09**	**m3/sn**	**27.06.2006**
2006 Su yılında anlık enaz akım	**:**	**0.000**	**m3/sn**	**01.10.2005**
Gözlem süresinde anlık ençok akım	**:**	**9.66**	**m3/sn**	**19.08.2002**
Gözlem süresinde anlık enaz akım	**:**	**0.000**	**m3/sn**	**08.08.1987**

Akımlar 01 Ekim 2005 'den 30 Eylül 2006' a kadar m3/sn olarak

Gün	Ekim	Kasım	Aralık	Ocak	Şubat	Mart	Nisan	Mayıs	Haziran	Temmuz	Ağustos	Eylül
01	KURU	0.034	0.092	0.056	0.170	0.215	0.320	0.170	0.170	0.170	0.056	0.007
02	0.005	0.034	0.092	0.056	0.170	0.215	0.320	0.170	0.170	0.056	0.056	0.033
03	0.005	0.034	0.092	0.056	0.170	0.215	0.320	0.170	0.215	0.056	0.056	0.033
04	0.005	0.034	0.092	0.056	0.170	0.215	0.320	0.320	0.265	0.056	0.056	0.033
05	0.005	0.056	0.034	0.056	0.170	0.215	0.320	0.320	0.086	0.056	0.056	0.033
06	0.005	0.056	0.015	0.092	0.170	0.215	0.320	0.320	0.033	0.056	0.033	0.014
07	0.005	0.034	0.015	0.092	0.215	0.170	0.320	0.265	0.033	0.056	0.033	0.033
08	0.005	0.015	0.015	0.092	0.215	0.215	0.265	0.265	0.033	0.056	0.056	0.033
09	0.005	0.015	0.015	0.092	0.215	0.170	0.265	0.265	0.033	0.056	0.056	0.014
10	0.005	0.015	0.015	0.092	0.215	0.170	0.265	0.265	0.033	0.056	0.056	0.033
11	0.005	0.034	0.015	0.092	0.215	0.170	0.265	0.265	0.033	0.056	0.056	0.033
12	0.446	0.034	0.015	0.092	0.320	0.170	0.265	0.265	0.033	0.056	0.056	0.056
13	0.015	0.056	0.015	0.092	0.320	0.380	0.215	0.265	0.033	0.056	0.014	0.033
14	0.034	0.092	0.015	0.092	0.320	0.684	0.215	0.215	0.033	0.056	0.033	0.033
15	0.034	0.092	0.015	0.092	0.320	0.748	0.265	0.215	0.033	0.056	0.056	0.056
16	0.034	0.092	0.015	0.092	0.320	0.812	0.215	0.215	0.033	0.033	0.014	0.056
17	0.034	0.092	0.015	0.092	0.320	0.812	0.215	0.170	0.033	0.033	0.033	0.056
18	0.034	0.130	0.015	0.092	0.320	0.876	0.215	0.170	0.033	0.056	0.033	0.056
19	0.015	0.092	0.056	0.092	0.320	0.876	0.215	0.170	0.033	0.056	0.033	0.056
20	0.015	0.092	0.092	0.092	0.320	0.876	0.215	0.170	0.033	0.056	0.033	0.056
21	0.015	0.092	0.092	0.092	0.215	0.876	0.215	0.170	0.033	0.056	0.033	0.056
22	0.015	0.092	0.092	0.092	0.215	0.876	0.215	0.170	0.033	0.056	0.033	0.056
23	0.015	0.092	0.092	0.092	0.215	0.876	0.265	0.170	0.033	0.056	0.014	0.086
24	0.015	0.092	0.092	0.130	0.215	0.876	0.320	0.170	0.033	0.056	0.033	0.125
25	0.015	0.092	0.056	0.130	0.215	0.876	0.265	0.170	0.033	0.056	0.033	0.086
26	0.015	0.092	0.056	0.215	0.215	0.684	0.265	0.170	0.033	0.056	0.014	0.033
27	0.015	0.092	0.056	0.215	0.215	0.560	0.215	0.170	0.265	0.056	0.014	0.033
28	0.015	0.092	0.056	0.215	0.215	0.500	0.170	0.170	1.01	0.056	0.033	0.033
29	0.015	0.092	0.056	0.170	-----	0.500	0.170	0.170	0.620	0.056	0.033	0.033
30	0.015	0.092	0.056	0.170	-----	0.500	0.170	0.170	0.320	0.056	0.014	0.033
31	0.015	-----	0.056	0.170	-----	0.440	-----	0.170	-----	0.056	0.033	-----
Maks.	0.446	0.559	0.264	0.218	0.440	1.07	0.684	0.500	3.09	1.01	0.125	0.170
Min.	KURU	0.005	0.015	0.056	0.125	0.170	0.170	0.086	0.014	0.033	0.007	0.007
Ortalama	0.028	0.068	0.049	0.108	0.239	0.516	0.253	0.210	0.127	0.058	0.037	0.044
LT/SN/Km2	0.819	1.98	1.41	3.13	6.93	14.9	7.35	6.10	3.69	1.69	1.09	1.29
AKIM mm.	2.19	5.14	3.77	8.39	16.8	40.0	19.0	16.3	9.55	4.52	2.91	3.33
MİL. M3	0.076	0.177	0.130	0.290	0.578	1.38	0.657	0.563	0.330	0.156	0.100	0.115

SU YILI (2006) YILLIK TOPLAM AKIM 4.55 MİLYON M3 132 MM. 4.2 LT/SN/Km2

08. Bati Akdeniz Havzasi

D08A106 ÇATALOLUK D. KARAÇULHA

YERİ : **KARAHASANTAŞI MAH.1KM SONRA SAĞA AYRILAN STABLİZE YOLDAN 2KM SONRAKİ BENGÜLDEK TEPE MEVKİİNDEDİR.**
29°38'39" Doğu - 36°56'47" Kuzey

YAĞIŞ ALANI : **8,00 km2** **YAKLAŞIK KOT : 1340 m**

GÖZLEM SÜRESİ : **01.10.1987 - 30.09.2006**

ORTALAMA AKIMLAR : **Gözlem süresinde 0.064 m3/sn. (3 Yıllık) 2006 Su yılında 0.064 m3/sn.**

ANLIK EN ÇOK VE EN AZ AKIMLAR:

2006 Su yılında anlık ençok akım	:	**5.75**	**m3/sn**	**26.06.2006**
2006 Su yılında anlık enaz akım	:	**0.001**	**m3/sn**	**18.10.2005**
Gözlem süresinde anlık ençok akım	:	**5.75**	**m3/sn**	**26.06.2006**
Gözlem süresinde anlık enaz akım	:	**0.001**	**m3/sn**	**01.10.1996**

Akımlar 01 Ekim 2005 'den 30 Eylül 2006' a kadar m3/sn olarak

Gün	Ekim	Kasım	Aralık	Ocak	Şubat	Mart	Nisan	Mayıs	Haziran	Temmuz	Ağustos	Eylül
01	0.064	0.001	0.001	0.001	0.064	0.150	0.150	0.250	0.001	0.150	0.010	0.001
02	0.064	0.001	0.001	0.001	0.064	0.150	0.150	0.250	0.001	0.150	0.010	0.001
03	0.064	0.001	0.001	0.001	0.064	0.150	0.150	0.250	0.001	0.150	0.010	0.001
04	0.064	0.001	0.001	0.001	0.064	0.150	0.150	0.250	0.001	0.150	0.010	0.001
05	0.064	0.001	0.001	0.001	0.064	0.150	0.064	0.250	0.001	0.150	0.010	0.001
06	0.064	0.001	0.001	0.001	0.064	0.150	0.064	0.250	0.001	0.150	0.010	0.001
07	0.064	0.001	0.001	0.010	0.064	0.150	0.064	0.250	0.001	0.150	0.001	0.001
08	0.064	0.001	0.001	0.010	0.064	0.150	0.064	0.250	0.001	0.150	0.001	0.001
09	0.064	0.001	0.001	0.010	0.064	0.064	0.064	0.250	0.001	0.150	0.001	0.001
10	0.064	0.001	0.001	0.010	0.064	0.064	0.064	0.250	0.001	0.150	0.001	0.001
11	0.064	0.001	0.001	0.010	0.250	0.064	0.064	0.250	0.001	0.150	0.001	0.001
12	0.064	0.001	0.001	0.010	0.250	0.064	0.064	0.250	0.001	0.010	0.001	0.001
13	0.064	0.001	0.001	0.010	0.250	0.064	0.064	0.250	0.001	0.010	0.001	0.001
14	0.064	0.001	0.001	0.010	0.250	0.064	0.064	0.250	0.001	0.010	0.001	0.001
15	0.064	0.001	0.001	0.010	0.250	0.064	0.064	0.250	0.001	0.010	0.001	0.001
16	0.064	0.001	0.001	0.010	0.150	0.064	0.250	0.250	0.001	0.010	0.001	0.001
17	0.064	0.001	0.001	0.010	0.150	0.064	0.250	0.250	0.001	0.010	0.001	0.001
18	0.001	0.001	0.001	0.010	0.150	0.150	0.250	0.250	0.001	0.010	0.001	0.001
19	0.001	0.001	0.001	0.010	0.150	0.150	0.250	0.250	0.001	0.010	0.001	0.001
20	0.001	0.010	0.010	0.010	0.150	0.150	0.250	0.250	0.001	0.010	0.001	0.001
21	0.001	0.010	0.010	0.010	0.150	0.150	0.250	0.250	0.001	0.010	0.001	0.001
22	0.001	0.010	0.010	0.010	0.150	0.150	0.250	0.250	0.010	0.010	0.001	0.001
23	0.001	0.010	0.010	0.010	0.150	0.150	0.250	0.250	0.010	0.010	0.001	0.001
24	0.001	0.001	0.010	0.010	0.150	0.150	0.250	0.250	0.010	0.010	0.001	0.001
25	0.001	0.001	0.001	0.010	0.150	0.150	0.250	0.064	0.010	0.010	0.001	0.001
26	0.001	0.001	0.001	0.010	0.150	0.150	0.250	0.001	0.250	0.010	0.001	0.001
27	0.001	0.001	0.001	0.064	0.150	0.150	0.250	0.001	0.150	0.010	0.001	0.001
28	0.001	0.001	0.001	0.064	0.150	0.150	0.250	0.001	0.150	0.010	0.001	0.001
29	0.001	0.001	0.001	0.064	-----	0.150	0.250	0.001	0.150	0.010	0.001	0.001
30	0.001	0.001	0.001	0.064	-----	0.150	0.250	0.001	0.150	0.010	0.001	0.001
31	0.001	-----	0.001	0.064	-----	0.150	-----	0.001	-----	0.010	0.001	-----
Maks.	0.064	0.150	0.064	0.250	1.10	0.250	0.360	0.250	5.75	0.250	0.010	0.001
Min.	0.001	0.001	0.001	0.001	0.001	0.064	0.064	0.001	0.001	0.010	0.001	0.001
Ortalama	0.036	0.002	0.002	0.017	0.137	0.125	0.168	0.196	0.030	0.060	0.003	0.001
LT/SN/Km2	4.44	0.275	0.306	2.12	17.1	15.6	21.1	24.5	3.80	7.46	0.343	0.125
AKIM mm.	11.9	0.713	0.821	5.68	41.5	41.9	54.6	65.6	9.84	20.0	0.918	0.324
MİL. M3	0.095	0.006	0.007	0.045	0.332	0.335	0.437	0.524	0.079	0.160	0.007	0.003

SU YILI (2006) YILLIK TOPLAM AKIM 2.03 MİLYON M3 254 MM. 8.0 LT/SN/Km2

08. Bati Akdeniz Havzasi

D08A108 SEKİ Ç. GACAK BOGAZI

YERİ : **FETHİYE ALTINYAYLA YOLUNUN 57.KM SİNDENDEN SOLA AHAT YAYLA MAH.AYRILAN YOLDAKİ KARAYOLU KÖPRÜSÜNÜN 1KM MANSABINDADIR..**
29°30'34" Doğu - 36°49'43" Kuzey

YAĞIŞ ALANI : **635,00 km2** **YAKLAŞIK KOT : 1050 m**

GÖZLEM SÜRESİ : **22.09.1987 - 30.09.2006**

ORTALAMA AKIMLAR : **Gözlem süresinde 3.052 m3/sn. (17 Yıllık) 2006 Su yılında 3.174 m3/sn.**

ANLIK EN ÇOK VE EN AZ AKIMLAR:

2006 Su yılında anlık ençok akım	**:**	**47.1**	**m3/sn**	**11.02.2006**
2006 Su yılında anlık enaz akım	**:**	**0.124**	**m3/sn**	**13.09.2006**
Gözlem süresinde anlık ençok akım	**:**	**409.**	**m3/sn**	**17.12.2002**
Gözlem süresinde anlık enaz akım	**:**	**0.035**	**m3/sn**	**30.08.1991**

Akımlar 01 Ekim 2005 'den 30 Eylül 2006' a kadar m3/sn olarak

Gün	Ekim	Kasım	Aralık	Ocak	Şubat	Mart	Nisan	Mayıs	Haziran	Temmuz	Ağustos	Eylül
01	0.147	0.464	0.924	1.03	1.85	5.68	10.9	7.60	1.23	1.77	0.303	0.147
02	0.361	0.464	0.873	1.03	1.85	5.00	10.1	7.36	1.13	1.54	0.303	0.171
03	0.669	0.515	0.822	1.03	1.77	5.00	9.85	6.88	1.03	1.62	0.303	0.171
04	0.515	0.617	0.822	1.03	1.69	4.79	10.1	7.12	0.873	1.69	0.303	0.171
05	0.464	0.566	0.822	0.975	1.62	4.39	9.85	7.36	0.873	2.94	0.303	0.171
06	0.515	0.566	0.822	0.975	2.12	4.39	9.35	6.88	0.873	2.47	0.275	0.171
07	0.515	0.566	0.822	0.975	8.35	4.59	9.85	6.40	0.771	2.12	0.275	0.171
08	0.515	0.515	0.822	0.924	6.40	7.60	10.1	5.92	0.669	1.77	0.275	0.171
09	0.464	0.515	0.873	0.924	4.79	6.88	9.85	5.68	0.720	1.38	0.275	0.171
10	0.412	0.515	0.873	0.873	6.16	5.44	9.10	5.20	0.720	1.08	0.246	0.147
11	0.412	0.515	0.873	0.873	39.5	5.20	8.85	5.00	0.720	1.03	0.246	0.147
12	0.412	0.464	0.771	0.822	31.8	5.68	8.85	4.59	0.720	0.873	0.246	0.147
13	0.361	0.464	0.771	0.822	13.6	10.1	9.10	4.59	0.720	0.771	0.217	0.147
14	0.412	0.515	0.822	0.873	9.10	25.6	9.60	4.19	0.720	0.771	0.217	0.124
15	0.412	0.515	0.924	0.924	6.88	19.5	12.4	3.78	0.771	0.720	0.217	0.124
16	0.412	0.515	0.822	0.924	5.92	15.9	15.4	3.78	0.822	0.720	0.194	0.147
17	0.464	0.566	1.03	0.924	5.44	13.4	12.6	3.78	0.720	0.720	0.217	0.171
18	0.464	0.873	2.47	0.924	8.10	12.9	11.6	3.37	0.720	0.720	0.217	0.171
19	0.464	1.13	6.88	1.38	6.64	12.4	10.1	3.17	0.669	0.669	0.194	0.171
20	0.464	4.19	2.59	6.64	5.68	11.4	9.85	2.94	0.669	0.617	0.194	0.194
21	0.464	1.77	1.77	3.17	5.44	11.4	9.10	2.70	0.669	0.566	0.194	0.194
22	0.464	1.38	1.54	3.05	5.00	11.4	8.85	2.47	0.669	0.566	0.194	0.194
23	0.464	1.18	1.31	3.37	4.79	11.1	9.85	2.12	0.720	0.515	0.194	0.194
24	0.464	1.08	1.13	3.37	4.79	11.6	11.4	1.85	0.669	0.515	0.194	0.246
25	0.464	1.03	1.13	8.35	4.59	11.6	9.60	1.69	0.669	0.515	0.171	0.464
26	0.464	0.975	1.08	4.39	4.79	11.1	8.85	1.62	0.873	0.464	0.171	0.515
27	0.464	0.975	1.08	2.94	5.00	11.4	8.35	1.62	1.69	0.412	0.171	0.515
28	0.464	0.975	1.13	2.59	4.39	11.4	8.35	1.54	2.70	0.361	0.171	0.515
29	0.464	0.924	1.13	2.23	-----	10.9	8.60	1.46	2.59	0.332	0.171	0.566
30	0.464	0.924	1.13	2.00	-----	10.4	8.10	1.38	2.12	0.332	0.147	0.566
31	0.464	-----	1.08	1.92	-----	11.4	-----	1.31	-----	0.332	0.147	-----
Maks.	0.771	7.60	8.10	11.6	47.1	30.9	17.1	7.60	4.39	3.58	0.303	0.566
Min.	0.147	0.464	0.771	0.822	1.54	4.39	7.85	1.31	0.617	0.332	0.147	0.124
Ortalama	0.450	0.875	1.29	2.01	7.43	9.99	9.95	4.04	0.984	0.997	0.224	0.239
LT/SN/Km2	0.709	1.38	2.03	3.16	11.7	15.7	15.7	6.37	1.55	1.57	0.353	0.377
AKIM mm.	1.90	3.57	5.43	8.47	28.3	42.1	40.6	17.1	4.02	4.20	0.945	0.976
MİL. M3	1.21	2.27	3.45	5.38	18.0	26.7	25.8	10.8	2.55	2.67	0.600	0.620

SU YILI (2006) YILLIK TOPLAM AKIM 100.05 MİLYON M3 158 MM. 5.0 LT/SN/Km2

08. Bati Akdeniz Havzasi

D08A112 KANLİGÖL D. KARACAHİSAR

YERİ : **MİLAS ÖREN KARAYOLUNDAN SAĞA AYRILAN KARACAHİSAR KÖYÜ KÖPRÜSÜN MENBASINDAN SOLA AYRILAN YOLUN 1.KM.SİNDEDİR..**
27°48'46" Doğu - 37°9'29" Kuzey

YAĞIŞ ALANI : **34,70 km2** **YAKLAŞIK KOT : 115 m**

GÖZLEM SÜRESİ : **20.12.1986 - 30.09.2006**

ORTALAMA AKIMLAR : **Gözlem süresinde 0.203 m3/sn. (9 Yıllık) 2006 Su yılında 0.203 m3/sn.**

ANLIK EN ÇOK VE EN AZ AKIMLAR:

2006 Su yılında anlık ençok akım	:	**28.0**	**m3/sn**	**26.11.2005**
2006 Su yılında anlık enaz akım	:	**0.005**	**m3/sn**	**02.11.2005**
Gözlem süresinde anlık ençok akım	:	**34.8**	**m3/sn**	**02.02.1998**
Gözlem süresinde anlık enaz akım	:	**0.005**	**m3/sn**	**27.09.1995**

Akımlar 01 Ekim 2005 'den 30 Eylül 2006' a kadar m3/sn olarak

Gün	Ekim	Kasım	Aralık	Ocak	Şubat	Mart	Nisan	Mayıs	Haziran	Temmuz	Ağustos	Eylül
01	0.088	0.008	0.262	0.185	0.185	0.319	0.234	0.123	0.102	0.144	0.102	0.102
02	0.291	0.005	0.262	0.185	0.185	0.206	0.206	0.144	0.074	0.144	0.102	0.102
03	0.061	0.008	0.262	0.185	0.185	0.206	0.185	0.144	0.088	0.123	0.102	0.102
04	0.061	0.033	0.262	0.164	0.185	0.185	0.164	0.164	0.123	0.144	0.102	0.102
05	0.061	0.022	0.262	0.347	0.185	0.206	0.164	0.144	0.102	0.123	0.102	0.102
06	0.061	0.022	0.234	0.291	1.05	0.206	0.144	0.144	0.102	0.123	0.102	0.102
07	0.061	0.033	0.234	0.234	1.94	0.500	0.144	0.144	0.088	0.123	0.102	0.102
08	0.061	0.088	0.234	0.206	0.500	0.627	0.144	0.144	0.088	0.123	0.102	0.102
09	0.061	0.033	0.234	0.206	0.319	0.385	0.185	0.144	0.102	0.123	0.102	0.102
10	0.061	0.033	0.262	0.164	0.262	0.319	0.206	0.123	0.102	0.123	0.102	0.102
11	0.074	0.022	0.234	0.144	0.291	0.291	0.144	0.144	0.164	0.123	0.102	0.102
12	0.061	0.022	0.234	0.144	0.319	0.385	0.185	0.144	0.164	0.102	0.102	0.102
13	0.047	0.015	0.234	0.144	0.262	4.10	0.185	0.144	0.164	0.102	0.102	0.102
14	0.047	0.033	0.234	0.144	0.206	2.50	0.185	0.123	0.164	0.102	0.102	0.102
15	0.047	0.033	0.347	0.144	0.206	0.934	0.185	0.123	0.164	0.102	0.102	0.102
16	0.047	0.033	0.206	0.144	0.206	0.877	0.185	0.144	0.164	0.102	0.102	0.102
17	0.047	0.061	0.206	0.102	0.234	0.761	0.164	0.144	0.164	0.102	0.102	0.102
18	0.047	0.627	0.291	0.123	0.234	0.716	0.144	0.123	0.144	0.102	0.102	0.102
19	0.047	0.262	0.672	0.144	0.206	0.627	0.144	0.123	0.144	0.102	0.102	0.102
20	0.047	0.164	0.262	0.164	0.234	0.583	0.185	0.123	0.144	0.102	0.102	0.102
21	0.047	0.102	0.206	0.144	0.206	0.262	0.164	0.123	0.123	0.102	0.102	0.102
22	0.033	0.088	0.185	0.144	0.185	0.262	0.144	0.088	0.123	0.102	0.102	0.102
23	0.033	0.144	0.185	0.206	0.164	0.234	0.123	0.074	0.123	0.102	0.102	0.185
24	0.033	0.123	0.185	0.262	0.164	0.185	0.123	0.074	0.123	0.102	0.102	0.164
25	0.047	0.123	0.164	0.672	0.164	0.234	0.144	0.074	0.123	0.102	0.102	0.144
26	0.061	7.12	0.144	0.262	0.164	0.234	0.123	0.074	0.123	0.102	0.102	0.102
27	0.061	0.423	0.164	0.206	0.164	0.206	0.144	0.088	0.123	0.102	0.102	0.102
28	0.033	0.319	0.164	0.185	0.206	0.234	0.144	0.074	0.144	0.102	0.102	0.102
29	0.022	0.262	0.185	0.185	-----	0.206	0.123	0.074	0.123	0.102	0.102	0.102
30	0.015	0.262	0.164	0.185	-----	0.206	0.123	0.074	0.144	0.102	0.102	0.102
31	0.010	-----	0.185	0.185	-----	0.234	-----	0.074	-----	0.102	0.102	-----
Maks.	3.73	28.0	4.90	4.80	14.3	16.5	0.291	0.319	0.185	0.206	0.102	0.185
Min.	0.010	0.005	0.144	0.102	0.164	0.185	0.123	0.047	0.074	0.102	0.102	0.102
Ortalama	0.057	0.351	0.237	0.200	0.315	0.562	0.161	0.118	0.127	0.111	0.102	0.108
LT/SN/Km2	1.65	10.1	6.84	5.76	9.07	16.2	4.65	3.39	3.67	3.21	2.94	3.12
AKIM mm.	4.41	26.2	18.3	15.4	21.9	43.4	12.0	9.07	9.52	8.61	7.87	8.08
MİL. M3	0.153	0.909	0.636	0.536	0.761	1.51	0.418	0.315	0.330	0.299	0.273	0.281

SU YILI (2006) YILLIK TOPLAM AKIM 6.42 MİLYON M3 185 MM. 5.9 LT/SN/Km2

08. Bati Akdeniz Havzasi

D08A134 ÇAYDERE BESİKCI

YERİ : **ANTALYA-KUMLUCA KARAYOLUNDAN GİDİLEREK 75 KM.DEN ESKİ KUMLUCA YOLUNA SAPILARAK GEÇMEDEN SOLA 300 M.GİDİLEREK İSTASYONA VARILIR.**
30°21'26" Doğu - 36°21'20" Kuzey

YAĞIŞ ALANI : **6,66 km2** **YAKLAŞIK KOT : 110 m**

GÖZLEM SÜRESİ : **01.10.1999 - 30.09.2006**

ORTALAMA AKIMLAR : **Gözlem süresinde 0.059 m3/sn. (7 Yıllık) 2006 Su yılında 0.031 m3/sn.**

ANLIK EN ÇOK VE EN AZ AKIMLAR:

2006 Su yılında anlık ençok akım	**:**	**2.76 m3/sn**	**23.01.2006**
2006 Su yılında anlık enaz akım	**:**	**0.000 m3/sn**	**01.10.2005**
Gözlem süresinde anlık ençok akım	**:**	**8.61 m3/sn**	**11.01.2004**
Gözlem süresinde anlık enaz akım	**:**	**0.000 m3/sn**	**01.10.1999**

Akımlar 01 Ekim 2005 'den 30 Eylül 2006' a kadar m3/sn olarak

Gün	Ekim	Kasım	Aralık	Ocak	Şubat	Mart	Nisan	Mayıs	Haziran	Temmuz	Ağustos	Eylül
01	KURU	KURU	0.001	0.002	0.100	0.072	0.050	0.050	0.005	KURU	KURU	KURU
02	KURU	KURU	0.001	0.002	0.072	0.072	0.050	0.050	0.005	KURU	KURU	KURU
03	KURU	KURU	0.001	0.002	0.072	0.072	0.050	0.050	0.005	KURU	KURU	KURU
04	KURU	KURU	0.001	0.001	0.050	0.072	0.050	0.030	0.005	KURU	KURU	KURU
05	KURU	KURU	0.001	0.001	0.050	0.072	0.050	0.030	0.005	KURU	KURU	KURU
06	KURU	KURU	0.001	0.005	0.072	0.072	0.050	0.030	0.005	KURU	KURU	KURU
07	KURU	KURU	0.001	0.002	0.167	0.072	0.050	0.030	0.005	KURU	KURU	KURU
08	KURU	KURU	0.001	0.002	0.133	0.072	0.050	0.020	0.005	KURU	KURU	KURU
09	KURU	KURU	0.001	0.002	0.100	0.072	0.050	0.020	0.005	KURU	KURU	KURU
10	KURU	KURU	0.001	0.002	0.100	0.072	0.050	0.020	0.005	KURU	KURU	KURU
11	KURU	KURU	0.001	0.002	0.250	0.072	0.050	0.020	0.005	KURU	KURU	KURU
12	KURU	KURU	0.001	0.002	0.400	0.072	0.050	0.010	0.005	KURU	KURU	KURU
13	KURU	KURU	0.001	0.002	0.250	0.100	0.050	0.010	0.001	KURU	KURU	KURU
14	KURU	KURU	0.001	0.002	0.200	0.167	0.050	0.010	0.001	KURU	KURU	KURU
15	KURU	KURU	0.001	0.001	0.167	0.133	0.050	0.010	0.001	KURU	KURU	KURU
16	KURU	KURU	0.002	0.001	0.167	0.100	0.050	0.010	0.001	KURU	KURU	KURU
17	KURU	KURU	0.001	0.001	0.133	0.100	0.050	0.010	0.001	KURU	KURU	KURU
18	KURU	KURU	0.020	0.001	0.133	0.072	0.050	0.005	KURU	KURU	KURU	KURU
19	KURU	KURU	0.005	0.005	0.133	0.072	0.050	0.005	KURU	KURU	KURU	KURU
20	KURU	KURU	0.001	0.020	0.100	0.072	0.050	0.005	KURU	KURU	KURU	KURU
21	KURU	KURU	0.001	0.010	0.100	0.072	0.050	0.005	KURU	KURU	KURU	KURU
22	KURU	KURU	0.001	0.010	0.100	0.072	0.050	0.005	KURU	KURU	KURU	KURU
23	KURU	KURU	0.001	0.750	0.100	0.072	0.050	0.005	KURU	KURU	KURU	KURU
24	KURU	KURU	0.001	0.975	0.100	0.050	0.050	0.005	KURU	KURU	KURU	KURU
25	KURU	KURU	0.001	0.675	0.100	0.050	0.050	0.005	KURU	KURU	KURU	KURU
26	KURU	0.001	0.001	0.400	0.072	0.050	0.050	0.005	KURU	KURU	KURU	KURU
27	KURU	0.001	0.001	0.200	0.072	0.072	0.050	0.005	KURU	KURU	KURU	KURU
28	KURU	0.001	0.050	0.072	0.072	0.072	0.050	0.005	KURU	KURU	KURU	KURU
29	KURU	0.001	0.020	0.020	-----	0.050	0.050	0.010	KURU	KURU	KURU	KURU
30	KURU	0.001	0.005	0.005	-----	0.050	0.050	0.010	KURU	KURU	KURU	KURU
31	0.001	-----	0.002	0.002	-----	0.050	-----	0.005	-----	KURU	KURU	-----
Maks.	0.001	0.001	0.200	2.76	1.13	0.900	0.050	0.133	0.020	KURU	KURU	KURU
Min.	KURU	KURU	KURU	0.001	0.050	0.050	0.050	0.002	KURU	KURU	KURU	KURU
Ortalama	0.000	0.000	0.004	0.102	0.127	0.075	0.050	0.016	0.002	KURU	KURU	KURU
LT/SN/Km2	0.005	0.025	0.620	15.4	19.1	11.3	7.51	2.37	0.325	0.000	0.000	0.000
AKIM mm.	0.013	0.065	1.66	41.2	46.2	30.4	19.5	6.36	0.843	0.000	0.000	0.000
MİL. M3	0.000	0.000	0.011	0.274	0.308	0.202	0.130	0.042	0.006	0.000	0.000	0.000

SU YILI (2006) YILLIK TOPLAM AKIM 0.97 MİLYON M3 146 MM. 4.6 LT/SN/Km2

08. Bati Akdeniz Havzasi

D08A135 KARABAYİR D. KARABAYİR

YERİ : **ANTALYA KORKUTELİ YOLUNDAN GIDILEREK KORKUTELI NE VARILIR.KORKUTELI ELMALI KARAYOLUNUN TAKRIBEN 20 KM SINDEKI KÖPRÜNÜN MENBAĞINDA 2 M. EŞELLİ OLARAK TESİS EDİLMİŞTİR. 30°3'43" Doğu - 36°55'6" Kuzey**

YAĞIŞ ALANI : **11,47 km2** **YAKLAŞIK KOT : 1292 m**

GÖZLEM SÜRESİ : **01.10.1999 - 30.09.2006**

ORTALAMA AKIMLAR : **Gözlem süresinde 0.033 m3/sn. (7 Yıllık) 2006 Su yılında 0.009 m3/sn.**

ANLIK EN ÇOK VE EN AZ AKIMLAR:

2006 Su yılında anlık ençok akım	:	**10.9**	**m3/sn**	**28.06.2006**
2006 Su yılında anlık enaz akım	:	**0.000**	**m3/sn**	**01.10.2005**
Gözlem süresinde anlık ençok akım	:	**12.9**	**m3/sn**	**13.07.2002**
Gözlem süresinde anlık enaz akım	:	**0.000**	**m3/sn**	**01.10.1999**

Akımlar 01 Ekim 2005 'den 30 Eylül 2006' a kadar m3/sn olarak

Gün	Ekim	Kasım	Aralık	Ocak	Şubat	Mart	Nisan	Mayıs	Haziran	Temmuz	Ağustos	Eylül
01	KURU	KURU	KURU	KURU	KURU	0.007	0.007	0.040	0.068	KURU	KURU	KURU
02	KURU	KURU	KURU	KURU	KURU	0.007	0.007	0.040	0.068	KURU	KURU	KURU
03	KURU	KURU	KURU	KURU	KURU	0.007	0.007	0.068	0.068	KURU	KURU	KURU
04	KURU	KURU	KURU	KURU	KURU	0.007	0.007	0.040	0.040	KURU	KURU	KURU
05	KURU	KURU	KURU	KURU	KURU	0.007	0.007	0.040	0.040	KURU	KURU	KURU
06	KURU	KURU	KURU	KURU	KURU	0.007	0.007	0.040	0.040	KURU	KURU	KURU
07	KURU	KURU	KURU	KURU	KURU	0.007	0.007	0.040	0.040	KURU	KURU	KURU
08	KURU	KURU	KURU	KURU	KURU	0.007	0.007	0.040	0.040	KURU	KURU	KURU
09	KURU	KURU	KURU	KURU	KURU	0.007	0.007	0.040	0.040	KURU	KURU	KURU
10	KURU	KURU	KURU	KURU	KURU	0.007	0.007	0.020	0.020	KURU	KURU	KURU
11	KURU	KURU	KURU	KURU	KURU	0.007	0.007	0.020	0.020	KURU	KURU	KURU
12	KURU	KURU	KURU	KURU	KURU	0.007	0.007	0.020	0.020	KURU	KURU	KURU
13	KURU	KURU	KURU	KURU	KURU	0.020	0.007	0.020	0.020	KURU	KURU	KURU
14	KURU	KURU	KURU	KURU	KURU	0.020	0.020	0.020	0.020	KURU	KURU	KURU
15	KURU	KURU	KURU	KURU	KURU	0.020	0.068	0.020	0.020	KURU	KURU	KURU
16	KURU	KURU	KURU	KURU	KURU	0.020	0.040	0.020	0.020	KURU	KURU	KURU
17	KURU	KURU	KURU	KURU	KURU	0.020	0.040	0.020	0.020	KURU	KURU	KURU
18	KURU	KURU	KURU	KURU	KURU	0.020	0.040	0.020	0.020	KURU	KURU	KURU
19	KURU	KURU	KURU	KURU	KURU	0.020	0.040	0.020	0.020	KURU	KURU	KURU
20	KURU	KURU	KURU	KURU	KURU	0.007	0.040	0.020	0.020	KURU	KURU	KURU
21	KURU	KURU	KURU	KURU	KURU	0.007	0.020	0.020	0.020	KURU	KURU	KURU
22	KURU	KURU	KURU	KURU	KURU	0.007	0.040	0.007	0.020	KURU	KURU	KURU
23	KURU	KURU	KURU	KURU	KURU	0.007	0.040	0.007	0.020	KURU	KURU	KURU
24	KURU	KURU	KURU	KURU	KURU	0.007	0.040	0.007	0.020	KURU	KURU	KURU
25	KURU	KURU	KURU	KURU	0.001	0.007	0.040	0.007	0.020	KURU	KURU	KURU
26	KURU	KURU	KURU	KURU	0.007	0.007	0.040	0.040	0.020	KURU	KURU	KURU
27	KURU	KURU	KURU	KURU	0.007	0.007	0.040	0.098	0.007	KURU	KURU	KURU
28	KURU	KURU	KURU	KURU	0.007	0.007	0.068	0.068	0.170	KURU	KURU	KURU
29	KURU	KURU	KURU	KURU	-----	0.007	0.040	0.068	0.001	KURU	KURU	KURU
30	KURU	KURU	KURU	KURU	-----	0.007	0.040	0.068	0.001	KURU	KURU	KURU
31	KURU	-----	KURU	KURU	-----	0.007	-----	0.068	-----	KURU	KURU	-----
Maks.	KURU	KURU	KURU	KURU	0.007	0.122	0.385	0.250	10.9	KURU	KURU	KURU
Min.	KURU	KURU	KURU	KURU	KURU	0.007	0.007	0.007	0.001	KURU	KURU	KURU
Ortalama	KURU	KURU	KURU	KURU	0.001	0.010	0.026	0.034	0.032	KURU	KURU	KURU
LT/SN/Km2	0.000	0.000	0.000	0.000	0.069	0.866	2.29	3.00	2.80	0.000	0.000	0.000
AKIM mm.	0.000	0.000	0.000	0.000	0.166	2.32	5.93	8.03	7.25	0.000	0.000	0.000
MİL. M3	0.000	0.000	0.000	0.000	0.002	0.027	0.068	0.092	0.083	0.000	0.000	0.000

SU YILI (2006) YILLIK TOPLAM AKIM 0.27 MİLYON M3 24 MM. 0.8 LT/SN/Km2

08. Bati Akdeniz Havzasi

D08A140 KARGICAK D. KÖYCEGİZ

YERİ : **KÖYCEĞİZ-AĞLA YOLUNUN 8.KM.SİNDEDİR.**
28°42'48" Doğu - 37°0'33" Kuzey

YAĞIŞ ALANI : **38,20 km2** **YAKLAŞIK KOT : 290 m**

GÖZLEM SÜRESİ : **01.10.2003 - 30.09.2006**

ORTALAMA AKIMLAR : **Gözlem süresinde 1.141 m3/sn. (3 Yıllık) 2006 Su yılında 1.167 m3/sn.**

ANLIK EN ÇOK VE EN AZ AKIMLAR:

2006 Su yılında anlık ençok akım	**:**	**18.5**	**m3/sn**	**26.02.2006**
2006 Su yılında anlık enaz akım	**:**	**0.000**	**m3/sn**	**01.10.2005**
Gözlem süresinde anlık ençok akım	**:**	**22.8**	**m3/sn**	**04.01.2004**
Gözlem süresinde anlık enaz akım	**:**	**0.000**	**m3/sn**	**01.10.2005**

Akımlar 01 Ekim 2005 'den 30 Eylül 2006' a kadar m3/sn olarak

Gün	Ekim	Kasım	Aralık	Ocak	Şubat	Mart	Nisan	Mayıs	Haziran	Temmuz	Ağustos	Eylül
01	0.200	0.427	0.626	0.884	1.40	3.32	2.08	1.14	0.712	0.540	0.464	0.427
02	0.884	0.389	0.626	0.884	1.31	3.10	1.91	1.06	0.626	0.540	0.464	0.427
03	0.626	0.464	0.626	0.884	1.31	3.10	1.74	1.06	0.626	0.540	0.464	0.427
04	0.502	0.502	0.626	0.798	1.31	3.10	1.74	1.06	0.626	0.540	0.464	0.427
05	0.464	0.464	0.626	0.884	1.23	2.93	1.74	1.06	0.626	0.712	0.464	0.427
06	0.427	0.464	0.626	1.14	6.38	2.76	1.74	1.06	0.712	0.626	0.464	0.427
07	0.427	0.464	0.626	0.970	4.64	2.59	1.74	0.970	0.712	0.626	0.464	0.427
08	0.389	0.464	0.626	0.884	4.64	3.76	1.57	0.970	0.712	0.540	0.464	0.427
09	0.389	0.427	0.626	0.884	3.76	3.32	1.57	0.884	0.712	0.540	0.464	0.427
10	0.389	0.427	0.626	0.798	3.10	3.32	1.57	0.884	0.712	0.540	0.464	0.427
11	0.389	0.427	0.626	0.798	3.32	3.10	1.40	0.884	0.712	0.502	0.464	0.427
12	0.427	0.427	0.626	0.798	3.10	3.54	1.40	0.884	0.712	0.502	0.464	0.427
13	0.389	0.427	0.798	0.798	2.76	5.08	1.40	0.884	0.712	0.502	0.464	0.427
14	0.389	0.427	0.798	0.798	2.42	10.1	1.40	0.884	0.712	0.502	0.464	0.427
15	0.389	0.427	0.884	0.798	2.08	7.19	1.40	0.884	0.712	0.502	0.464	0.427
16	0.389	0.427	0.884	0.798	1.91	6.11	1.40	0.884	0.712	0.502	0.464	0.427
17	0.389	0.464	0.798	0.798	1.91	5.30	1.31	0.884	0.626	0.502	0.464	0.427
18	0.427	1.14	1.91	0.798	2.25	5.08	1.31	0.884	0.626	0.502	0.464	0.427
19	0.427	0.884	4.42	0.798	2.08	4.64	1.31	0.970	0.540	0.464	0.464	0.427
20	0.427	0.970	1.40	0.798	1.91	4.42	1.23	0.884	0.540	0.464	0.464	0.427
21	0.427	0.798	1.06	0.970	1.74	4.20	1.23	0.884	0.540	0.464	0.464	0.427
22	0.427	0.798	0.970	1.14	1.57	3.98	1.23	0.884	0.540	0.464	0.464	0.427
23	0.427	0.712	0.884	1.06	1.57	3.98	1.23	0.884	0.540	0.464	0.464	0.427
24	0.389	0.712	0.884	2.25	1.74	3.76	1.23	0.798	0.540	0.464	0.427	0.464
25	0.389	0.712	0.884	4.20	1.91	3.54	1.23	0.798	0.502	0.464	0.427	0.464
26	0.389	0.712	0.884	3.10	3.10	3.32	1.23	0.798	0.502	0.464	0.427	0.464
27	0.389	0.626	0.884	2.25	3.32	3.32	1.14	0.798	0.884	0.464	0.427	0.464
28	0.389	0.626	0.798	1.91	3.10	3.10	1.14	0.798	0.884	0.464	0.427	0.464
29	0.389	0.626	1.14	1.74	-----	2.93	1.14	0.712	0.712	0.464	0.427	0.464
30	0.389	0.626	0.970	1.57	-----	2.59	1.14	0.712	0.626	0.464	0.427	0.464
31	0.389	-----	0.970	1.40	-----	2.08	-----	0.712	-----	0.464	0.427	-----
Maks.	14.9	3.76	8.90	4.20	18.5	16.1	2.25	1.23	4.64	1.57	0.626	0.540
Min.	KURU	0.389	0.502	0.798	1.23	1.91	0.970	0.712	0.502	0.464	0.427	0.427
Ortalama	0.424	0.582	0.959	1.24	2.53	3.96	1.43	0.898	0.655	0.509	0.454	0.436
LT/SN/Km2	11.1	15.2	25.1	32.6	66.3	104.	37.4	23.5	17.1	13.3	11.9	11.4
AKIM mm.	29.7	39.5	67.2	87.3	160.	277.	97.0	63.0	44.4	35.7	31.9	29.6
MİL. M3	1.13	1.51	2.57	3.33	6.12	10.6	3.71	2.41	1.70	1.36	1.22	1.13

SU YILI (2006) YILLIK TOPLAM AKIM 36.79 MİLYON M3 963 MM. 30.5 LT/SN/Km2

08. Bati Akdeniz Havzasi

D08A143 KOCAÇAY ÖREN MİLAS

YERİ : **ÖREN -ALATEPE YOLUNUN 6.KM.SİNDEDİR..**
27°59'46" Doğu - 37°4'9" Kuzey

YAĞIŞ ALANI : **247,40 km2** **YAKLAŞIK KOT : 83 m**

GÖZLEM SÜRESİ : **01.10.2004 - 30.09.2006**

ORTALAMA AKIMLAR : **Gözlem süresinde 1.119 m3/sn. (1 Yıllık) 2006 Su yılında 1.119 m3/sn.**

ANLIK EN ÇOK VE EN AZ AKIMLAR:

2006 Su yılında anlık ençok akım	**:**	**44.0**	**m3/sn**	**26.11.2005**
2006 Su yılında anlık enaz akım	**:**	**0.000**	**m3/sn**	**30.07.2006**
Gözlem süresinde anlık ençok akım	**:**	**44.0**	**m3/sn**	**26.11.2005**
Gözlem süresinde anlık enaz akım	**:**	**0.000**	**m3/sn**	**30.07.2006**

Akımlar 01 Ekim 2005 'den 30 Eylül 2006' a kadar m3/sn olarak

Gün	Ekim	Kasım	Aralık	Ocak	Şubat	Mart	Nisan	Mayıs	Haziran	Temmuz	Ağustos	Eylül
01	0.060	0.006	0.448	1.42	1.42	4.40	1.42	0.448	0.060	0.001	KURU	KURU
02	0.160	0.006	0.376	1.26	1.42	2.30	1.42	0.448	0.025	0.001	KURU	KURU
03	0.100	0.006	0.232	0.984	1.10	2.10	1.26	0.376	0.025	0.001	KURU	KURU
04	0.006	0.006	0.232	0.868	1.10	1.90	1.10	0.376	0.025	0.001	KURU	KURU
05	0.006	0.006	0.160	1.10	0.984	1.74	1.10	0.376	0.025	0.001	KURU	KURU
06	0.006	0.006	0.160	1.74	2.30	1.58	0.984	0.376	0.025	KURU	KURU	KURU
07	0.006	0.006	0.160	1.10	4.76	1.90	0.984	0.304	0.025	KURU	KURU	KURU
08	0.006	0.006	0.160	0.984	4.76	11.0	0.984	0.304	0.025	KURU	KURU	KURU
09	0.006	0.006	0.100	0.868	2.50	8.00	0.868	0.304	0.025	KURU	KURU	KURU
10	0.006	0.006	0.100	0.868	3.50	5.12	0.868	0.304	0.025	KURU	KURU	KURU
11	0.006	0.006	0.060	0.868	6.80	4.10	0.868	0.304	0.025	KURU	KURU	KURU
12	0.006	0.006	0.060	0.752	7.70	7.70	0.752	0.304	0.025	KURU	KURU	KURU
13	0.006	0.006	0.060	0.636	4.40	15.5	0.752	0.304	0.025	KURU	KURU	KURU
14	0.006	0.006	0.060	0.636	3.50	20.8	0.984	0.232	0.025	KURU	KURU	KURU
15	0.006	0.006	2.10	0.636	2.90	9.20	1.42	0.232	0.025	KURU	KURU	KURU
16	0.006	0.006	0.520	0.636	2.50	7.40	0.984	0.232	0.025	KURU	KURU	KURU
17	0.006	0.025	0.304	0.520	2.70	6.20	0.868	0.232	0.025	KURU	KURU	KURU
18	0.006	4.10	0.984	0.520	4.40	5.12	0.752	0.232	0.025	KURU	KURU	KURU
19	0.006	0.520	13.9	0.752	4.10	4.40	0.752	0.160	0.025	KURU	KURU	KURU
20	0.006	2.90	2.50	7.10	4.76	3.80	0.636	0.160	0.025	KURU	KURU	KURU
21	0.006	0.448	1.42	2.10	3.50	3.20	0.636	0.160	0.025	KURU	KURU	KURU
22	0.006	0.232	0.984	1.58	2.90	2.90	0.636	0.160	0.025	KURU	KURU	KURU
23	0.006	0.160	0.868	6.50	2.50	2.70	0.636	0.100	0.025	KURU	KURU	KURU
24	0.006	0.868	0.752	6.80	2.30	2.30	0.520	0.100	0.025	KURU	KURU	KURU
25	0.006	0.376	0.636	9.20	2.30	2.30	0.520	0.100	0.025	KURU	KURU	KURU
26	0.006	14.8	0.520	4.76	2.10	2.10	0.520	0.100	0.006	KURU	KURU	KURU
27	0.006	2.50	0.636	3.20	2.10	1.90	0.448	0.060	0.001	KURU	KURU	KURU
28	0.006	0.984	0.984	2.70	1.90	1.74	0.448	0.060	0.001	KURU	KURU	KURU
29	0.006	0.636	9.80	2.30	-----	1.74	0.448	0.060	0.001	KURU	KURU	KURU
30	0.006	0.520	2.90	1.90	-----	1.58	0.448	0.060	0.001	KURU	KURU	KURU
31	0.006	-----	1.74	1.58	-----	1.42	-----	0.060	-----	KURU	KURU	-----
Maks.	1.26	44.0	42.6	28.2	11.3	41.1	1.90	0.448	0.376	0.001	KURU	KURU
Min.	0.001	0.006	0.060	0.520	0.984	1.42	0.448	0.060	0.001	KURU	KURU	KURU
Ortalama	0.016	0.972	1.42	2.16	3.11	4.78	0.834	0.227	0.022	0.000	KURU	KURU
LT/SN/Km2	0.064	3.93	5.73	8.72	12.6	19.3	3.37	0.916	0.090	0.001	0.000	0.000
AKIM mm.	0.170	10.2	15.3	23.4	30.5	51.7	8.74	2.45	0.234	0.002	0.000	0.000
MİL. M3	0.042	2.52	3.79	5.78	7.53	12.8	2.16	0.607	0.058	0.000	0.000	0.000

SU YILI (2006) YILLIK TOPLAM AKIM 35.29 MİLYON M3 143 MM. 4.5 LT/SN/Km2

08. Bati Akdeniz Havzasi

D08A144 AKDERE ÖRENKÖY (ACİPAYAM)

YERİ : **ACIPAYAM-ÇAKIR KÖYE 2KM.KALA SAĞA AYRILAN ÇUBUKÇULAR YOLUN 4.KM SİNDEDİR.**
29°18'10" Doğu - 37°19'38" Kuzey

YAĞIŞ ALANI : **69,10 km2** **YAKLAŞIK KOT : 900 m**

GÖZLEM SÜRESİ : **12.05.1998 - 30.09.2006**

ORTALAMA AKIMLAR : **Gözlem süresinde 0.353 m3/sn. (1 Yıllık) 2006 Su yılında 0.353 m3/sn.**

ANLIK EN ÇOK VE EN AZ AKIMLAR:

2006 Su yılında anlık ençok akım	:	**4.06**	**m3/sn**	**07.08.2006**
2006 Su yılında anlık enaz akım	:	**0.002**	**m3/sn**	**01.10.2005**
Gözlem süresinde anlık ençok akım	:	**4.06**	**m3/sn**	**07.08.2006**
Gözlem süresinde anlık enaz akım	:	**0.002**	**m3/sn**	**01.10.2005**

Akımlar 01 Ekim 2005 'den 30 Eylül 2006' a kadar m3/sn olarak

Gün	Ekim	Kasım	Aralık	Ocak	Şubat	Mart	Nisan	Mayıs	Haziran	Temmuz	Ağustos	Eylül
01	0.002	0.009	0.088	0.400	0.400	0.840	0.982	0.664	0.400	0.344	0.288	0.070
02	0.004	0.009	0.088	0.400	0.400	0.840	0.982	0.664	0.232	0.344	0.288	0.070
03	0.007	0.009	0.088	0.400	0.400	0.840	0.840	0.488	0.176	0.344	0.288	0.070
04	0.007	0.009	0.088	0.400	0.400	0.840	0.840	0.400	0.176	0.344	0.232	0.070
05	0.007	0.009	0.047	0.232	0.400	0.840	0.840	0.488	0.176	0.232	0.232	0.070
06	0.007	0.009	0.033	0.176	0.400	0.664	0.664	0.488	0.176	0.120	0.232	0.070
07	0.007	0.009	0.033	0.232	0.488	0.664	0.664	0.488	0.176	0.120	0.120	0.070
08	0.007	0.009	0.033	0.232	0.664	0.664	0.576	0.488	0.176	0.120	0.070	0.070
09	0.007	0.009	0.033	0.232	0.576	0.664	0.576	0.488	0.176	0.120	0.070	0.070
10	0.007	0.009	0.033	0.232	0.488	0.664	0.576	0.488	0.176	0.088	0.070	0.070
11	0.007	0.009	0.033	0.232	0.488	0.664	0.576	0.488	0.176	0.088	0.070	0.070
12	0.007	0.009	0.033	0.232	0.664	0.840	0.576	0.488	0.176	0.088	0.070	0.070
13	0.009	0.009	0.033	0.232	0.664	1.12	0.576	0.488	0.176	0.088	0.070	0.070
14	0.009	0.009	0.033	0.232	0.664	1.89	0.576	0.488	0.176	0.088	0.070	0.070
15	0.009	0.020	0.033	0.232	0.664	1.89	0.576	0.488	0.176	0.088	0.070	0.070
16	0.009	0.020	0.033	0.232	0.576	1.89	0.576	0.488	0.176	0.120	0.070	0.070
17	0.009	0.020	0.033	0.232	0.576	2.06	0.576	0.488	0.176	0.088	0.070	0.070
18	0.009	0.232	0.033	0.232	0.576	2.06	0.488	0.488	0.176	0.120	0.070	0.070
19	0.009	0.088	1.41	0.176	0.576	2.06	0.488	0.488	0.176	0.120	0.070	0.070
20	0.009	0.288	0.840	0.120	0.488	2.06	0.488	0.488	0.176	0.120	0.070	0.070
21	0.009	0.120	0.664	0.176	0.400	2.06	0.488	0.488	0.176	0.120	0.070	0.070
22	0.009	0.120	0.576	0.176	0.400	2.23	0.488	0.400	0.176	0.120	0.070	0.070
23	0.009	0.120	0.488	0.176	0.400	2.60	0.488	0.400	0.176	0.288	0.070	0.070
24	0.009	0.088	0.488	0.176	0.400	2.06	0.664	0.400	0.176	0.288	0.070	0.070
25	0.009	0.088	0.488	0.576	0.488	1.89	0.664	0.400	0.232	0.288	0.070	0.070
26	0.009	0.088	0.400	0.576	0.488	1.55	0.664	0.400	0.344	0.288	0.070	0.070
27	0.009	0.088	0.400	0.488	0.840	1.55	0.664	0.400	0.344	0.288	0.070	0.070
28	0.009	0.088	0.400	0.400	0.840	1.55	0.664	0.400	0.344	0.288	0.070	0.070
29	0.009	0.088	0.400	0.400	-----	1.27	0.664	0.400	0.344	0.288	0.070	0.070
30	0.009	0.088	0.400	0.400	-----	1.12	0.664	0.400	0.344	0.288	0.070	0.070
31	0.009	-----	0.400	0.400	-----	1.12	-----	0.400	-----	0.288	0.070	-----
Maks.	0.344	2.23	2.80	0.664	0.840	3.00	1.12	0.664	2.23	1.27	4.06	0.232
Min.	0.002	0.009	0.020	0.088	0.400	0.576	0.488	0.400	0.088	0.070	0.002	0.033
Ortalama	0.008	0.059	0.264	0.291	0.529	1.39	0.638	0.468	0.215	0.194	0.108	0.070
LT/SN/Km2	0.115	0.854	3.82	4.22	7.65	20.1	9.24	6.77	3.11	2.81	1.57	1.01
AKIM mm.	0.309	2.21	10.2	11.3	18.5	53.8	23.9	18.1	8.07	7.52	4.20	2.63
MİL. M3	0.021	0.153	0.707	0.780	1.28	3.72	1.65	1.25	0.558	0.520	0.290	0.181

SU YILI (2006) YILLIK TOPLAM AKIM 11.11 MİLYON M3 161 MM. 5.1 LT/SN/Km2

09

ANTALYA HAVZASI

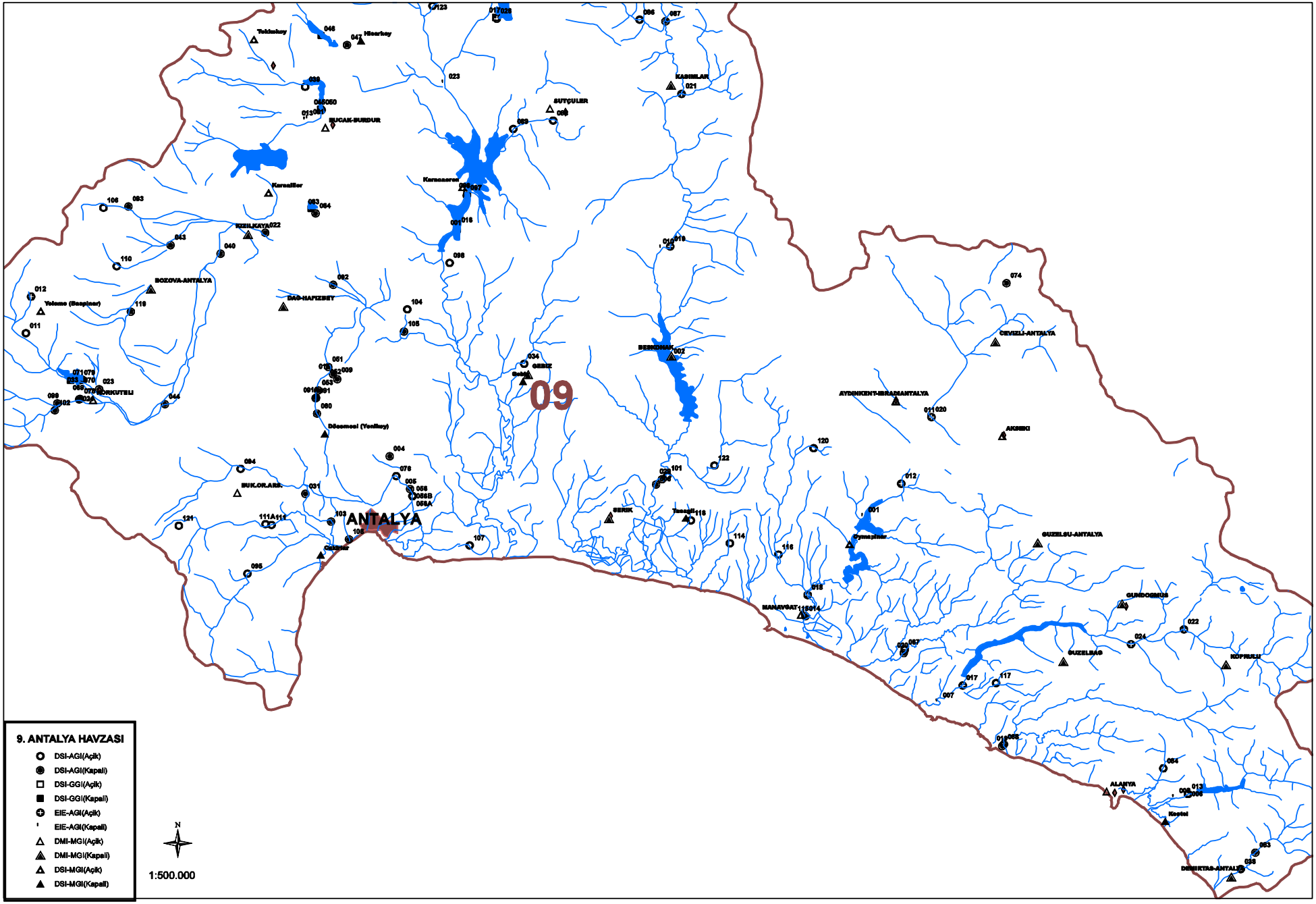
09
ANTALYA
9. ANTALYA HAVZASI
DSI-AGI(Açik)
DSI-AGI(Kapali)
DSI-GGI(Açik)
DSI-GGI(Kapali)
EIE-AGI(Açik)
EIE-AGI(Kapali)
DMI-MGI(Açik)
DMI-MGI(Kapali)
DSI-MGI(Açik)
DSI-MGI(Kapali)
N
1:500.000

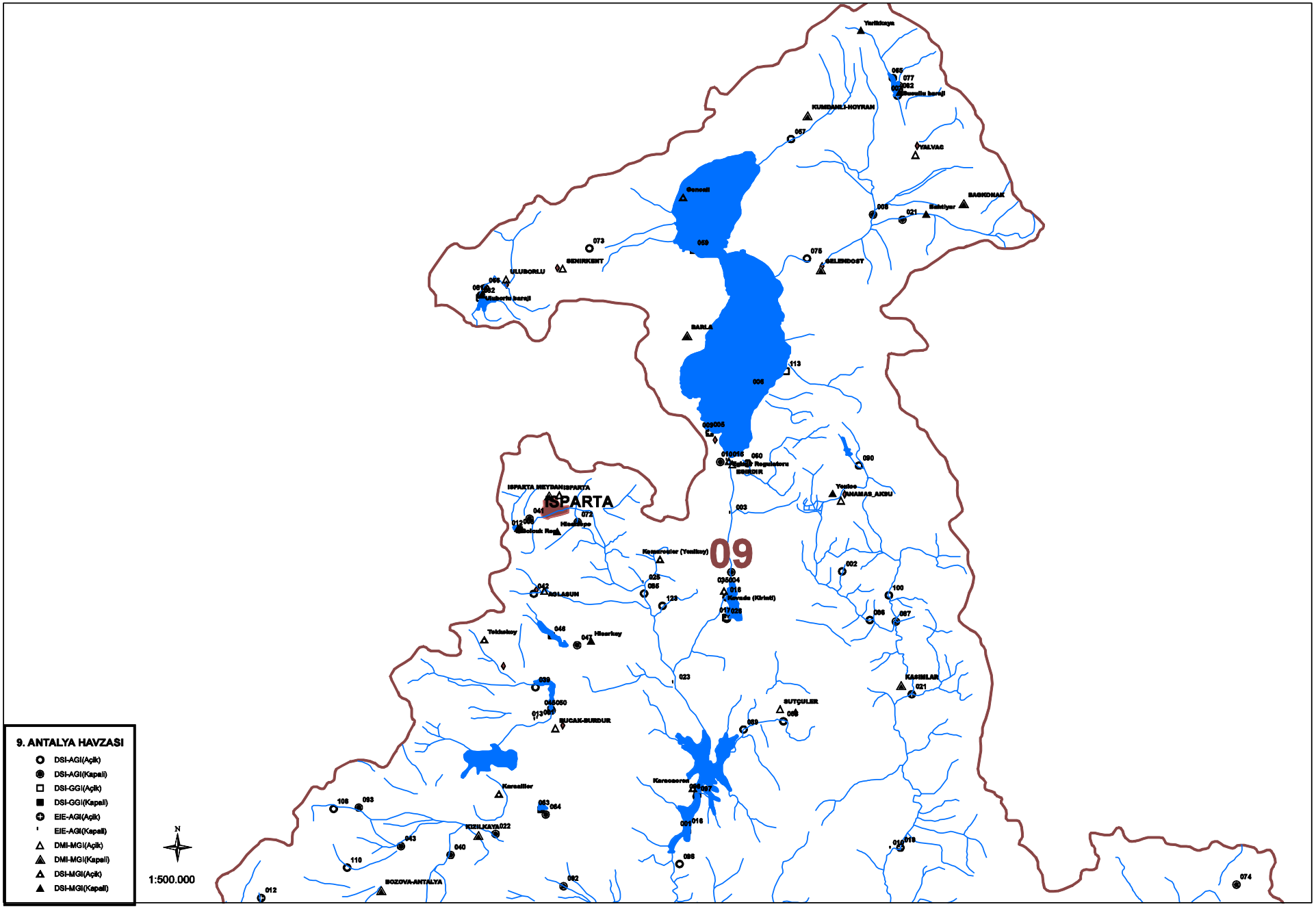
9. ANTALYA HAVZASI
DSI-AGI(Açik)
DSI-AGI(Kapali)
DSI-GGI(Açik)
DSI-GGI(Kapali)
EIE-AGI(Açik)
EIE-AGI(Kapali)
DMI-MGI(Açik)
DMI-MGI(Kapali)
DSI-MGI(Açik)
DSI-MGI(Kapali)
N
1:500.000
09
ISPARTA
Yarlikaya
KUMBANLI-HOYRAN
YALVAC
BAGKONAK
Gencali
SENIRKENT
ULUBORLU
GELENDOST
BARLA
ERMENK
ANAMAS_AKDU
Kesmeveiler (Yenikoy)
AGLASUN
Tekkeköy
Hisarköy
KASIMLAR
SUTÇULER
BUCAK-BURDUR
Karaalilar
KIZILKAYA
BOZOVA-ANTALYA

09. Antalya Havzasi

D09A002 YENİCE S. ZİNDAN BOĞAZI

YERİ : ISPARTA AKSU İLÇESİNE VARILIR. ZİNDAN MAĞARASI YOLUNA GİRİLEREK YENİCE SUYU ÜZERİNDE SAĞ SAHİLDEDİR. HARİTA PAFTA NO: M26-A4
31°5'27" Doğu - 37°42'42" Kuzey

YAĞIŞ ALANI : 61,70 km2 YAKLAŞIK KOT : 1250 m

GÖZLEM SÜRESİ : 30.05.1958 - 30.09.2006

ORTALAMA AKIMLAR : Gözlem süresinde 2.899 m3/sn. (45 Yıllık) 2006 Su yılında 3.002 m3/sn.

ANLIK EN ÇOK VE EN AZ AKIMLAR:

2006 Su yılında anlık ençok akım	:	10.7	m3/sn	08.04.2006
2006 Su yılında anlık enaz akım	:	0.700	m3/sn	01.10.2005
Gözlem süresinde anlık ençok akım	:	105.	m3/sn	16.12.1981
Gözlem süresinde anlık enaz akım	:	0.000	m3/sn	01.01.1978

9. Anahtar Eğrisi (Seviyeler cm olarak)

Seviye	Akım	Seviye	Akım	Seviye	Akım	Seviye	Akım
27	0.010	42	0.700	68	6.2	130	56.0
30	0.042	45	0.965	90	15.0	140	72.0
33	0.125	48	1.3	100	22.0	150	88.0
36	0.270	52	1.8	110	32.0	160	100.
39	0.450	60	3.7	120	42.0	170	120.

Akımlar 01 Ekim 2005 'den 30 Eylül 2006' a kadar m3/sn olarak

Gün	Ekim	Kasım	Aralık	Ocak	Şubat	Mart	Nisan	Mayıs	Haziran	Temmuz	Ağustos	Eylül
01	0.700	0.965	0.877	0.965	0.788	2.97	9.04	7.36	3.20	1.85	2.28	3.20
02	0.788	0.965	0.877	0.965	0.788	2.97	8.76	7.36	3.20	1.85	2.28	2.97
03	0.877	0.965	0.877	0.965	0.788	4.50	8.76	7.36	3.20	1.85	2.28	2.73
04	0.877	0.965	0.877	0.965	0.788	5.83	8.76	7.08	2.97	1.85	2.28	2.50
05	0.877	0.965	0.877	0.965	0.788	4.80	8.20	7.08	3.20	1.85	2.28	2.28
06	0.877	0.965	0.877	1.08	0.877	4.20	8.76	7.08	3.20	1.70	2.50	2.28
07	0.877	0.965	0.877	1.19	0.877	5.47	9.32	6.80	3.20	1.70	2.50	2.07
08	0.877	0.965	0.877	1.19	0.877	5.47	10.7	6.80	3.20	1.85	2.50	2.07
09	0.877	0.965	0.877	1.19	0.965	4.50	10.1	6.80	3.20	1.85	2.73	2.28
10	0.788	0.965	0.877	1.19	1.08	3.95	9.04	6.80	3.20	2.07	2.73	2.28
11	0.788	0.877	0.877	1.19	1.08	3.95	8.48	6.50	2.97	2.28	2.73	2.07
12	0.788	0.877	0.877	1.19	1.08	4.80	8.48	6.50	2.97	2.28	2.73	2.07
13	0.788	0.877	0.877	1.08	2.07	5.10	8.48	6.50	2.97	2.28	2.73	2.07
14	1.55	0.877	0.877	1.08	2.97	5.47	8.20	6.50	2.97	2.28	2.73	2.07
15	3.20	0.877	0.877	0.965	2.28	5.47	8.20	6.50	2.97	2.28	2.73	2.07
16	3.45	0.877	0.877	0.965	1.70	5.47	8.20	6.20	2.97	2.07	3.20	2.07
17	3.70	0.877	0.877	0.965	1.43	5.47	8.48	5.83	2.97	2.07	3.20	2.07
18	3.70	0.877	0.877	0.965	1.30	5.47	8.20	5.10	2.97	2.07	3.20	2.07
19	3.95	0.877	0.877	0.965	1.19	5.83	8.76	5.10	2.73	2.07	3.20	2.07
20	3.95	0.877	0.877	0.965	1.08	5.83	8.76	4.80	2.73	2.07	3.20	2.07
21	3.95	0.877	0.877	0.965	0.965	5.83	7.92	4.80	2.73	2.28	3.20	2.07
22	3.95	0.877	0.877	0.877	0.965	6.50	7.92	4.50	2.73	2.28	3.20	2.07
23	3.95	0.877	0.965	0.877	0.965	7.92	7.92	4.50	2.73	2.50	3.20	2.07
24	3.95	0.877	0.965	0.877	1.19	7.92	7.92	4.50	2.50	2.50	3.20	1.70
25	3.95	0.877	0.965	0.877	1.30	7.36	7.92	4.50	2.50	2.50	3.20	1.19
26	2.28	0.877	0.965	0.877	1.55	7.36	7.92	4.50	2.28	2.28	3.20	1.08
27	0.965	0.877	0.965	0.877	2.97	7.08	7.92	4.50	2.07	2.28	3.20	0.965
28	0.965	0.877	0.965	0.877	2.97	7.08	7.92	4.20	2.07	2.28	3.20	0.877
29	0.965	0.877	0.965	0.877	-----	8.48	7.92	3.70	1.85	2.28	3.20	0.877
30	0.965	0.877	0.965	0.788	-----	8.76	7.92	3.45	1.85	2.28	3.20	0.788
31	0.965	-----	0.965	0.788	-----	9.60	-----	3.20	-----	2.28	3.20	-----
Maks.	3.95	0.965	0.965	1.19	2.97	9.60	10.7	7.36	3.20	2.50	3.20	3.20
Min.	0.700	0.877	0.877	0.788	0.788	2.97	7.92	3.20	1.85	1.70	2.28	0.788
Ortalama	1.97	0.906	0.903	0.986	1.35	5.85	8.50	5.69	2.81	2.13	2.88	1.97
LT/SN/Km2	32.0	14.7	14.6	16.0	21.8	94.8	138.	92.2	45.5	34.5	46.6	31.9
AKIM mm.	85.6	38.1	39.2	42.8	52.8	254.	357.	247.	118.	92.3	125.	82.7
MİL. M3	5.28	2.35	2.42	2.64	3.25	15.7	22.0	15.2	7.28	5.69	7.71	5.10

SU YILI (2006) YILLIK TOPLAM AKIM 94.62 MİLYON M3 1534 MM. 48.7 LT/SN/Km2

09. Antalya Havzasi

D09A006 DİM Ç. SAG SAHİL SUL.KAN.

YERİ : ALANYA GAZİPAŞA SAHİL YOLUNUN 5.KM SİNDEN SOLA AYRILAN DİM BİRLİK YOLUNUN 7 5 KM SİNDEKİ REGÜLATÖRÜN SAĞ SAHİL SULAMASINDAKİ KANALDADIR. (EŞELLİ) 32°7'18" Doğu - 36°32'58" Kuzey

YAĞIŞ ALANI : 195,00 km2 YAKLAŞIK KOT : 38 m

GÖZLEM SÜRESİ : 31.05.1958 - 30.09.2006

ORTALAMA AKIMLAR : Gözlem süresinde 0.884 m3/sn. (41 Yıllık) 2006 Su yılında 0.955 m3/sn.

ANLIK EN ÇOK VE EN AZ AKIMLAR:

2006 Su yılında anlık ençok akım	:	2.04	m3/sn	10.11.2005
2006 Su yılında anlık enaz akım	:	0.043	m3/sn	24.11.2005
Gözlem süresinde anlık ençok akım	:	3.50	m3/sn	13.01.1995
Gözlem süresinde anlık enaz akım	:	0.000	m3/sn	15.04.1986

9. Anahtar Eğrisi (Seviyeler cm olarak)

Seviye	Akım	Seviye	Akım	Seviye	Akım	Seviye	Akım
1	0.000	42	0.210	82	0.740	122	1.4
9	0.014	50	0.290	90	0.860	130	1.6
18	0.046	58	0.390	98	1.0	142	1.8
26	0.090	66	0.500	106	1.2	150	2.0
34	0.145	74	0.610	114	1.2	196	3.0

Akımlar 01 Ekim 2005 'den 30 Eylül 2006' a kadar m3/sn olarak

Gün	Ekim	Kasım	Aralık	Ocak	Şubat	Mart	Nisan	Mayıs	Haziran	Temmuz	Ağustos	Eylül
01	1.09	1.30	0.043	0.530	0.055	0.098	1.25	1.35	1.49	1.66	1.58	1.60
02	1.09	1.35	0.170	0.043	0.047	0.092	0.840	1.35	1.47	1.66	1.58	1.66
03	1.09	0.959	0.810	0.220	0.310	0.620	0.125	1.30	1.45	1.66	1.58	1.47
04	1.08	0.052	0.810	0.043	1.08	1.17	0.125	1.30	1.45	1.66	1.58	1.35
05	1.08	0.052	0.800	0.043	0.700	0.760	0.120	1.25	1.43	1.64	1.51	1.35
06	1.06	0.052	0.480	0.180	0.060	0.125	0.120	1.25	1.43	1.64	1.51	1.30
07	1.06	0.310	0.043	0.760	0.120	0.125	0.400	1.19	1.43	1.64	1.51	1.30
08	1.06	1.58	0.043	0.450	0.120	0.125	1.30	0.730	1.41	1.62	1.51	1.35
09	1.03	1.60	0.250	0.043	0.120	0.125	0.999	0.130	1.40	1.62	1.47	1.35
10	1.01	1.64	1.35	0.043	0.120	0.270	0.130	0.125	1.40	1.62	1.47	1.35
11	1.15	1.35	1.35	0.043	0.240	1.04	0.130	0.150	1.35	1.62	1.47	1.25
12	1.17	1.35	1.35	0.043	0.390	0.660	0.130	0.972	1.35	1.64	1.73	1.30
13	1.15	0.900	1.30	0.210	0.081	0.130	0.760	1.49	1.35	1.64	1.73	1.30
14	1.14	0.052	1.30	0.959	0.076	0.150	1.45	1.54	1.35	1.66	1.70	1.30
15	1.14	0.055	0.340	0.630	0.070	0.155	1.45	1.51	1.35	1.66	1.70	1.25
16	1.19	0.060	0.150	0.043	0.070	0.155	0.830	1.49	1.35	1.70	1.70	1.30
17	1.60	0.065	0.810	0.043	0.065	0.360	0.130	1.49	1.35	1.70	1.47	1.30
18	1.56	0.076	0.490	0.043	0.530	1.41	0.120	1.45	1.47	1.70	1.47	1.25
19	1.86	0.690	0.081	0.043	0.630	0.900	0.120	1.45	1.66	1.70	1.66	1.25
20	1.93	1.19	0.055	0.300	0.125	0.165	0.120	1.45	1.70	1.73	1.66	1.19
21	1.77	0.830	0.052	0.999	0.110	0.165	1.03	1.47	1.70	1.75	1.64	1.25
22	1.62	0.092	0.052	0.640	0.105	0.165	1.47	1.49	1.70	1.75	1.58	1.35
23	1.51	0.065	0.170	0.065	0.105	0.165	1.47	1.51	1.70	1.77	1.60	1.35
24	1.40	0.047	0.900	0.076	0.092	0.490	1.43	1.54	1.70	1.77	1.60	1.03
25	1.35	0.180	0.870	0.098	0.560	1.49	1.41	1.56	1.68	1.66	1.60	0.620
26	1.30	0.860	0.570	0.092	0.760	0.830	1.35	1.51	1.68	1.66	1.51	0.620
27	1.25	0.480	0.043	0.290	0.120	0.130	1.35	1.51	1.75	1.70	1.51	0.610
28	1.25	0.170	0.043	1.11	0.120	0.120	1.35	1.51	1.73	1.58	1.51	0.610
29	1.19	0.972	0.043	0.690	-----	0.110	1.35	1.51	1.68	1.58	1.51	0.800
30	1.20	0.340	0.170	0.086	-----	0.105	1.40	1.51	1.68	1.56	1.45	1.03
31	1.20	-----	0.830	0.070	-----	0.690	-----	1.49	-----	1.56	1.45	-----
Maks.	1.98	2.04	1.35	1.14	1.18	1.79	1.54	1.60	1.79	1.82	1.77	1.86
Min.	0.870	0.043	0.043	0.043	0.047	0.092	0.110	0.060	1.35	1.56	1.45	0.610
Ortalama	1.28	0.624	0.509	0.288	0.249	0.422	0.809	1.28	1.52	1.66	1.57	1.20
LT/SN/Km2	6.55	3.20	2.61	1.48	1.28	2.17	4.15	6.55	7.80	8.52	8.03	6.16
AKIM mm.	17.5	8.29	6.99	3.96	3.09	5.80	10.7	17.5	20.2	22.8	21.5	16.0
MİL. M3	3.42	1.62	1.36	0.771	0.603	1.13	2.10	3.42	3.94	4.45	4.19	3.11

SU YILI (2006) YILLIK TOPLAM AKIM 30.11 MİLYON M3 154 MM. 4.9 LT/SN/Km2

09. Antalya Havzasi

D09A011 KORKUTELİ Ç. SALAMUR BOG.

YERİ : **KORKUTELİ-SÜLEKLER KÖY YOLUNUN 16.KM.SINDEKI BOĞAZDADIR.**
30°3'0" Doğu - 37°8'0" Kuzey

YAĞIŞ ALANI : 130,70 km2 **YAKLAŞIK KOT :** 1190 m

GÖZLEM SÜRESİ : 11.05.1959 - **30.09.2006**

ORTALAMA AKIMLAR : Gözlem süresinde 1.007 m3/sn. (43 Yıllık) 2006 Su yılında 0.443 m3/sn.

ANLIK EN ÇOK VE EN AZ AKIMLAR:

2006 Su yılında anlık ençok akım	:	**3.48**	**m3/sn**	**05.05.2006**
2006 Su yılında anlık enaz akım	:	**0.060**	**m3/sn**	**16.07.2006**
Gözlem süresinde anlık ençok akım	:	**53.0**	**m3/sn**	**02.11.1967**
Gözlem süresinde anlık enaz akım	:	**0.000**	**m3/sn**	**11.06.1990**

Akımlar 01 Ekim 2005 'den 30 Eylül 2006' a kadar m3/sn olarak

Gün	Ekim	Kasım	Aralık	Ocak	Şubat	Mart	Nisan	Mayıs	Haziran	Temmuz	Ağustos	Eylül
01	0.465	0.465	0.555	0.420	0.510	0.555	0.600	0.715	0.375	0.420	0.240	0.240
02	0.465	0.465	0.555	0.420	0.510	0.555	0.600	0.830	0.420	0.330	0.240	0.240
03	0.510	0.465	0.510	0.420	0.510	0.555	0.555	1.06	0.420	0.330	0.240	0.195
04	0.465	0.465	0.510	0.420	0.510	0.555	0.555	1.18	0.420	0.465	0.240	0.195
05	0.510	0.465	0.510	0.420	0.510	0.510	0.600	2.83	0.420	0.600	0.240	0.195
06	0.510	0.465	0.510	0.420	0.510	0.510	0.600	0.945	0.420	0.510	0.285	0.195
07	0.510	0.465	0.555	0.420	0.510	0.510	0.600	0.715	0.375	0.465	0.195	0.195
08	0.510	0.465	0.510	0.420	0.555	0.510	0.600	0.600	0.375	0.465	0.195	0.240
09	0.510	0.465	0.555	0.420	0.510	0.555	0.600	0.600	0.375	0.375	0.195	0.195
10	0.510	0.465	0.555	0.420	0.510	0.510	0.600	0.555	0.375	0.285	0.195	0.240
11	0.510	0.465	0.555	0.420	0.510	0.510	0.600	0.555	0.420	0.195	0.195	0.240
12	0.510	0.465	0.555	0.420	0.555	0.510	0.600	0.555	0.330	0.195	0.195	0.285
13	0.510	0.465	0.555	0.420	0.555	0.555	0.600	0.555	0.330	0.195	0.195	0.240
14	0.510	0.465	0.510	0.420	0.555	0.715	0.600	0.555	0.330	0.150	0.195	0.240
15	0.510	0.510	0.510	0.420	0.510	0.715	0.600	0.555	0.330	0.105	0.195	0.195
16	0.510	0.510	0.555	0.420	0.510	0.715	0.715	0.555	0.330	0.150	0.195	0.150
17	0.510	0.510	0.555	0.420	0.510	0.715	0.600	0.465	0.330	0.105	0.195	0.150
18	0.510	0.510	0.420	0.420	0.510	0.555	0.600	0.420	0.330	0.150	0.330	0.150
19	0.510	0.510	0.420	0.420	0.510	0.510	0.600	0.375	0.330	0.150	0.285	0.150
20	0.510	0.510	0.420	0.420	0.510	0.555	0.600	0.375	0.330	0.195	0.240	0.150
21	0.510	0.510	0.420	0.420	0.555	0.510	0.600	0.375	0.330	0.375	0.195	0.150
22	0.510	0.510	0.420	0.420	0.555	0.510	0.600	0.420	0.285	0.285	0.195	0.150
23	0.510	0.510	0.420	0.420	0.510	0.510	0.715	0.375	0.285	0.240	0.195	0.150
24	0.465	0.510	0.420	0.420	0.510	0.510	0.830	0.375	0.240	0.240	0.240	0.195
25	0.510	0.510	0.420	0.555	0.510	0.555	0.715	0.375	0.240	0.195	0.240	0.285
26	0.510	0.510	0.420	0.510	0.555	0.555	0.715	0.465	0.285	0.195	0.240	0.285
27	0.510	0.510	0.420	0.510	0.555	0.600	0.715	0.465	0.285	0.195	0.195	0.330
28	0.510	0.510	0.420	0.510	0.555	0.715	0.715	0.420	0.285	0.195	0.195	0.330
29	0.510	0.510	0.420	0.510	-----	0.600	0.715	0.420	0.285	0.195	0.240	0.330
30	0.465	0.510	0.420	0.510	-----	0.600	0.715	0.420	0.375	0.195	0.195	0.330
31	0.465	-----	0.420	0.510	-----	0.600	-----	0.375	-----	0.195	0.195	-----
Maks.	0.510	0.600	0.555	0.600	0.600	0.830	0.945	3.48	0.420	3.29	0.420	0.330
Min.	0.465	0.465	0.420	0.375	0.510	0.510	0.555	0.375	0.240	0.060	0.150	0.150
Ortalama	0.501	0.489	0.484	0.442	0.524	0.569	0.635	0.628	0.342	0.269	0.220	0.221
LT/SN/Km2	3.84	3.74	3.70	3.38	4.01	4.35	4.86	4.81	2.62	2.06	1.68	1.69
AKIM mm.	10.3	9.70	9.92	9.05	9.71	11.7	12.6	12.9	6.78	5.51	4.50	4.37
MİL. M3	1.34	1.27	1.30	1.18	1.27	1.52	1.65	1.68	0.886	0.721	0.588	0.572

SU YILI (2006) YILLIK TOPLAM AKIM 13.98 MİLYON M3 107 MM. 3.4 LT/SN/Km2

09. Antalya Havzasi

D09A013 DİM Ç. REG.ÇİKIS

YERİ : **ALANYA-GAZİPAŞA YOLUNDA ÜZÜMLÜ KÖY YOLUNDAKI REGÜLATÖRDEDIR.**
32°7'18" Doğu - 36°32'58" Kuzey

YAĞIŞ ALANI : 195,00 km2 **YAKLAŞIK KOT :** 33 m

GÖZLEM SÜRESİ : **01.08.1960 - 30.09.2006**

ORTALAMA AKIMLAR : Gözlem süresinde 14.114 m3/sn. (45 Yıllık) 2006 Su yılında 10.318 m3/sn.

ANLIK EN ÇOK VE EN AZ AKIMLAR:

2006 Su yılında anlık ençok akım	:	89.4	m3/sn	12.02.2006
2006 Su yılında anlık enaz akım	:	0.020	m3/sn	07.10.2005
Gözlem süresinde anlık ençok akım	:	620.	m3/sn	06.01.1981
Gözlem süresinde anlık enaz akım	:	0.000	m3/sn	25.10.2001

Akımlar 01 Ekim 2005 'den 30 Eylül 2006' a kadar m3/sn olarak

Gün	Ekim	Kasım	Aralık	Ocak	Şubat	Mart	Nisan	Mayıs	Haziran	Temmuz	Ağustos	Eylül
01	0.074	0.055	4.50	3.35	9.46	14.5	32.4	20.5	9.98	2.01	0.172	0.133
02	0.055	0.035	4.01	3.84	9.46	14.3	34.5	20.0	9.72	1.80	0.152	0.152
03	0.028	0.191	3.35	3.68	8.42	13.8	36.0	19.5	9.20	1.80	0.152	0.152
04	0.028	3.18	3.35	4.01	7.33	13.8	35.0	17.0	8.94	1.71	0.133	0.133
05	0.035	2.85	3.35	4.01	7.33	14.8	32.8	15.5	8.68	1.71	0.113	0.133
06	0.035	2.54	3.18	4.50	9.20	14.3	29.0	14.8	8.42	1.61	0.113	0.133
07	0.035	1.80	3.18	4.34	37.5	14.8	26.0	14.0	7.90	1.61	0.113	0.152
08	0.035	0.664	3.18	4.34	47.4	20.0	27.0	14.5	7.14	1.52	0.113	0.152
09	0.035	0.664	2.54	4.50	43.2	27.5	28.0	15.5	6.57	0.850	0.133	0.152
10	0.035	0.664	1.71	4.50	43.8	21.0	30.8	14.8	5.70	1.23	0.133	0.172
11	0.113	0.788	1.52	4.17	72.0	16.0	31.2	14.5	5.10	1.14	0.113	0.152
12	0.035	0.726	1.42	4.17	72.0	14.3	32.0	14.5	4.95	0.850	0.113	0.113
13	0.028	0.945	1.33	3.51	65.5	17.5	32.4	15.0	4.80	0.945	0.113	0.113
14	0.028	2.01	1.14	2.64	45.0	32.0	30.8	16.5	4.65	0.850	0.113	0.113
15	0.028	2.12	2.12	2.64	35.5	41.4	33.6	14.8	4.65	0.788	0.113	0.094
16	0.035	2.01	2.43	3.02	29.5	33.6	43.8	14.0	4.50	0.726	0.113	0.094
17	0.074	2.01	3.02	3.02	24.0	29.0	49.2	13.3	4.17	0.602	0.152	0.094
18	0.074	3.18	16.5	3.02	18.0	24.5	42.0	12.5	4.01	0.540	0.133	0.094
19	0.094	9.98	38.5	3.84	14.8	36.5	34.5	12.5	3.68	0.416	0.113	0.113
20	0.074	14.0	34.5	25.5	14.5	34.0	36.0	12.3	3.51	0.416	0.113	0.094
21	0.094	17.0	22.5	14.0	14.5	30.8	35.0	12.8	3.18	0.292	0.113	0.094
22	0.094	13.3	12.8	9.98	14.5	28.0	31.2	12.8	2.85	0.664	0.094	0.152
23	0.074	10.5	9.72	10.5	14.5	29.0	30.4	13.5	2.85	0.664	0.094	0.172
24	0.055	6.76	6.95	11.9	14.3	33.2	28.5	14.3	2.75	0.664	0.113	0.788
25	0.055	4.65	5.55	36.0	13.8	43.8	25.5	14.0	2.54	0.602	0.113	2.01
26	0.055	3.51	5.10	41.4	14.5	39.0	21.5	13.0	2.54	0.478	0.113	1.80
27	0.055	3.51	5.10	26.5	16.0	36.5	19.0	12.3	3.68	0.416	0.113	1.33
28	0.035	4.01	4.80	14.5	16.5	34.5	19.5	11.7	3.02	0.191	0.113	1.23
29	0.035	3.68	4.80	11.9	-----	35.0	18.0	11.3	2.54	0.191	0.113	0.788
30	0.035	4.65	4.34	11.3	-----	35.0	22.5	10.9	2.33	0.191	0.113	0.478
31	0.035	-----	3.35	10.5	-----	34.0	-----	10.5	-----	0.191	0.113	-----
Maks.	2.75	19.5	55.0	49.2	89.4	61.6	53.0	22.0	10.5	2.33	0.191	3.18
Min.	0.020	0.035	1.14	2.54	7.14	13.5	17.0	9.98	2.33	0.191	0.094	0.094
Ortalama	0.052	4.07	7.09	9.52	26.2	26.7	30.9	14.3	5.15	0.892	0.120	0.379
LT/SN/Km2	0.265	20.9	36.4	48.8	134.	137.	159.	73.3	26.4	4.58	0.616	1.95
AKIM mm.	0.709	54.0	97.4	131.	325.	366.	411.	196.	68.5	12.3	1.65	5.04
MİL. M3	0.138	10.5	19.0	25.5	63.3	71.4	80.2	38.3	13.4	2.39	0.321	0.983

SU YILI (2006) YILLIK TOPLAM AKIM 325.43 MİLYON M3 1669 MM. 52.9 LT/SN/Km2

09. Antalya Havzasi

D09A016 KOVADA G. ÇİKIS

YERİ : **EĞİRDİR-KEPEZ HİDROELEKTİRİK SANTRALİ YOLUNUN 2. KM SİNDE KOVADA GÖLÜ ÇIKIŞINDADIR**

30°52'0" Doğu - 37°39'0" Kuzey

YAĞIŞ ALANI : **3728,00 km2** **YAKLAŞIK KOT : 903 m**

GÖZLEM SÜRESİ : **01.04.1962 - 30.09.2006**

ORTALAMA AKIMLAR : Gözlem süresinde 9.171 m3/sn. (35 Yıllık) 2006 Su yılında 2.323 m3/sn.

ANLIK EN ÇOK VE EN AZ AKIMLAR:

2006 Su yılında anlık ençok akım	:	7.96	m3/sn	31.03.2006
2006 Su yılında anlık enaz akım	:	0.162	m3/sn	27.12.2005
Gözlem süresinde anlık ençok akım	:	46.0	m3/sn	10.03.1984
Gözlem süresinde anlık enaz akım	:	0.000	m3/sn	07.06.1975

10. Anahtar Eğrisi (Seviyeler cm olarak)

Akımlar 01 Ekim 2005 'den 30 Eylül 2006' a kadar m3/sn olarak

Gün	Ekim	Kasım	Aralık	Ocak	Şubat	Mart	Nisan	Mayıs	Haziran	Temmuz	Ağustos	Eylül
01	0.342	0.230	3.40	0.162	5.24	4.88	7.84	3.63	2.64	0.308	0.354	2.86
02	0.342	0.230	3.27	0.162	5.06	4.79	7.60	3.63	0.354	0.308	0.354	2.80
03	0.370	0.230	3.20	0.162	4.88	4.97	7.40	3.63	0.354	0.308	0.354	2.69
04	0.370	0.286	3.13	0.162	4.70	4.97	7.20	3.63	0.354	0.308	0.354	2.59
05	0.370	0.286	3.06	0.179	4.53	4.88	7.00	3.63	0.354	0.308	0.354	2.48
06	0.342	0.286	2.99	0.179	4.88	4.79	6.80	3.63	0.354	0.308	0.354	2.38
07	0.342	0.258	2.92	0.179	4.70	4.79	7.60	3.63	0.331	0.308	0.354	2.32
08	0.314	0.230	2.78	0.179	5.15	4.88	7.40	3.63	0.331	0.308	0.354	2.32
09	0.314	0.196	2.64	0.179	5.15	4.97	7.20	3.63	0.308	0.308	0.354	2.27
10	0.314	0.196	2.71	0.179	5.15	5.06	7.00	3.56	0.308	0.308	0.354	2.27
11	0.314	0.196	0.196	0.179	5.15	5.15	5.50	3.49	0.308	0.308	0.354	2.22
12	0.314	0.196	0.196	0.162	5.51	5.15	5.35	3.42	0.308	0.308	0.354	2.22
13	0.314	0.196	0.179	0.162	7.60	5.51	5.20	3.35	0.285	0.308	0.354	2.18
14	0.314	0.196	0.179	0.162	7.72	6.20	5.13	3.30	0.308	0.308	0.354	2.18
15	0.314	0.196	0.179	0.162	7.40	7.10	5.05	3.30	0.308	0.308	0.354	2.13
16	0.314	0.196	0.179	0.162	7.30	7.10	4.75	3.24	0.308	0.308	0.354	0.354
17	0.342	0.196	0.179	0.162	7.20	7.10	4.47	3.24	3.02	0.308	0.354	0.354
18	0.342	0.213	0.179	0.162	7.50	7.00	4.19	3.24	2.91	0.308	0.354	0.331
19	0.342	0.213	0.213	0.162	7.40	7.00	3.98	3.19	2.80	0.308	0.400	0.331
20	3.94	0.213	0.213	0.162	7.30	7.00	3.77	3.19	2.75	0.308	0.400	0.331
21	3.85	0.213	0.213	0.162	0.342	7.40	3.56	3.13	2.64	0.308	0.377	0.331
22	3.72	0.213	0.196	0.179	0.342	7.30	4.26	3.08	2.59	2.75	0.354	0.354
23	3.53	4.45	0.196	0.179	0.370	7.50	4.05	3.02	2.48	2.59	0.354	0.354
24	3.40	4.28	0.196	0.179	0.400	7.30	3.91	2.97	2.43	2.43	0.354	0.331
25	3.20	4.11	0.196	0.196	0.430	7.20	3.70	2.91	2.38	2.27	0.354	0.331
26	3.06	3.94	0.179	0.196	0.520	7.30	3.49	2.86	2.32	2.22	3.24	0.331
27	2.85	3.79	0.162	0.196	5.15	7.40	3.35	2.86	2.27	0.643	3.13	0.331
28	2.71	3.72	0.162	0.196	4.97	7.40	3.35	2.80	0.308	0.400	3.08	3.35
29	0.258	3.66	0.162	5.24	-----	7.40	3.63	2.80	0.308	0.400	3.02	3.30
30	0.258	3.53	0.162	5.06	-----	7.40	3.49	2.75	0.308	0.354	2.97	3.24
31	0.230	-----	0.162	4.88	-----	7.96	-----	2.69	-----	0.354	2.91	-----
Maks.	3.94	4.45	3.40	5.24	7.72	7.96	7.84	3.63	3.02	2.75	3.24	3.35
Min.	0.230	0.196	0.162	0.162	0.342	4.79	3.24	2.69	0.285	0.308	0.354	0.331
Ortalama	1.20	1.21	1.10	0.646	4.72	6.29	5.24	3.26	1.23	0.674	0.881	1.66
LT/SN/Km2	0.323	0.325	0.294	0.173	1.26	1.69	1.41	0.874	0.331	0.181	0.236	0.446
AKIM mm.	0.865	0.842	0.787	0.464	3.06	4.52	3.64	2.34	0.858	0.484	0.633	1.16
MİL. M3	3.23	3.14	2.94	1.73	11.4	16.8	13.6	8.73	3.20	1.80	2.36	4.31

SU YILI (2006) YILLIK TOPLAM AKIM 73.24 MİLYON M3 20 MM. 0.6 LT/SN/Km2

09. Antalya Havzasi

D09A031 KARAMAN Ç. KAPUZ BOG.

YERİ : ANTALYADAN DURALILER KÖYÜNE VARILIR.ORADAN AŞAĞI KARAMAN KÖYÜ IÇINDEN MEZARLIĞA GELİNCE SAĞ YOL TAKIP EDILEREK 2KM.SONRA ISTASYONA VARILIR.
30°34'25" Doğu - 36°56'5" Kuzey

YAĞIŞ ALANI : 404,60 km2 YAKLAŞIK KOT : 52 m

GÖZLEM SÜRESİ : 01.10.1963 - 30.09.2006

ORTALAMA AKIMLAR : Gözlem süresinde 2.537 m3/sn. (6 Yıllık) 2006 Su yılında 1.327 m3/sn.

ANLIK EN ÇOK VE EN AZ AKIMLAR:

2006 Su yılında anlık ençok akım	:	26.5	m3/sn	14.03.2006
2006 Su yılında anlık enaz akım	:	0.000	m3/sn	23.07.2006
Gözlem süresinde anlık ençok akım	:	419.	m3/sn	11.01.2004
Gözlem süresinde anlık enaz akım	:	0.000	m3/sn	03.07.2003

Akımlar 01 Ekim 2005 'den 30 Eylül 2006' a kadar m3/sn olarak

Gün	Ekim	Kasım	Aralık	Ocak	şubat	Mart	Nisan	Mayıs	Haziran	Temmuz	Ağustos	Eylül
01	0.931	1.11	0.931	2.32	2.55	2.32	2.90	1.66	0.253	0.253	KURU	KURU
02	1.29	0.749	0.931	2.02	2.55	2.32	2.90	1.66	0.253	0.253	KURU	KURU
03	1.84	0.931	0.931	1.84	2.55	2.32	2.90	1.66	0.253	0.253	KURU	KURU
04	1.84	1.11	2.02	1.84	2.43	2.32	3.01	1.66	0.253	0.332	KURU	KURU
05	1.84	1.11	2.20	1.84	2.43	2.32	2.90	1.84	0.253	0.410	KURU	KURU
06	1.84	1.11	2.20	1.84	2.43	2.20	1.84	1.84	0.253	0.410	KURU	KURU
07	1.84	1.11	2.20	1.84	2.43	2.02	1.84	1.84	0.332	0.332	KURU	KURU
08	1.66	1.11	2.02	1.84	3.13	2.02	1.84	1.66	0.332	0.292	KURU	KURU
09	1.47	1.11	1.66	1.84	3.13	2.20	1.84	1.66	0.332	0.213	KURU	KURU
10	1.11	1.11	1.66	1.84	2.55	2.20	1.84	1.66	0.332	0.213	KURU	KURU
11	1.11	0.931	1.66	1.84	2.55	2.20	1.84	2.02	0.332	0.213	KURU	KURU
12	1.11	0.931	1.66	2.02	2.32	2.20	1.84	2.02	0.371	0.253	KURU	KURU
13	1.11	1.11	1.66	2.02	1.84	3.13	1.84	2.02	0.410	0.253	KURU	KURU
14	1.11	1.11	1.66	2.02	1.84	7.00	1.84	1.66	0.450	0.332	KURU	KURU
15	1.11	1.11	1.66	2.02	1.29	4.13	1.84	1.66	0.489	0.410	KURU	KURU
16	1.11	0.931	1.66	2.02	2.78	3.36	3.24	1.66	0.371	0.174	KURU	KURU
17	1.84	1.11	1.66	2.02	2.66	3.24	2.20	1.66	0.253	0.134	KURU	KURU
18	2.66	1.11	1.66	2.02	2.55	3.24	1.66	1.66	0.253	0.134	KURU	KURU
19	2.20	1.11	1.84	2.02	2.55	3.01	1.66	1.47	0.253	0.134	KURU	KURU
20	2.02	1.11	2.02	2.02	2.55	3.01	1.66	1.47	0.253	0.134	KURU	KURU
21	2.32	1.11	2.20	2.02	2.55	3.01	1.66	1.29	0.253	0.144	KURU	KURU
22	1.66	1.11	2.20	2.02	2.55	3.01	1.66	1.29	0.253	0.104	KURU	KURU
23	0.931	1.29	2.20	3.36	2.55	3.01	1.84	1.29	0.253	KURU	KURU	KURU
24	1.47	1.11	2.20	4.70	2.55	3.01	1.84	0.931	0.253	KURU	KURU	KURU
25	1.47	0.931	2.20	3.36	2.55	3.01	1.66	0.568	0.253	KURU	KURU	KURU
26	0.931	0.931	2.02	3.36	2.55	3.01	1.66	0.568	0.253	KURU	KURU	0.292
27	0.931	0.931	2.02	2.78	2.55	3.01	1.66	0.489	0.213	KURU	KURU	0.292
28	1.29	0.931	2.43	2.66	2.55	3.01	1.66	0.253	0.213	KURU	KURU	0.292
29	1.47	0.931	2.43	2.66	-----	3.01	1.66	0.253	0.253	KURU	KURU	0.332
30	1.47	0.931	2.32	2.66	-----	2.90	1.66	0.253	0.213	KURU	KURU	0.213
31	1.29	-----	2.32	2.66	-----	2.90	-----	0.253	-----	KURU	KURU	-----
Maks.	2.90	2.02	2.78	5.66	7.57	26.5	7.00	4.13	1.47	0.410	KURU	0.332
Min.	0.749	0.749	0.931	1.84	1.29	2.02	1.66	0.253	0.134	KURU	KURU	KURU
Ortalama	1.49	1.04	1.88	2.30	2.48	2.89	2.01	1.35	0.290	0.174	KURU	0.047
LT/SN/Km2	3.69	2.58	4.66	5.69	6.14	7.15	4.98	3.34	0.716	0.429	0.000	0.117
AKIM mm.	9.88	6.69	12.5	15.2	14.8	19.1	12.9	8.94	1.86	1.15	0.000	0.303
MİL. M3	4.00	2.71	5.05	6.16	6.01	7.75	5.22	3.62	0.751	0.465	0.000	0.123

SU YILI (2006) YILLIK TOPLAM AKIM 41.86 MİLYON M3 103 MM. 3.3 LT/SN/Km2

09. Antalya Havzasi

D09A034 KÜÇÜKAKSU . GEBİZ

YERİ : **ANTALYA SERİK YOLUNUN 22. KM.SINDE SOLA AYRILAN GEBIZ YOLUNU25 KM.ILERISINDEKI GEBIZ ILÇESININ 3 KM.ILERDEKI AKSU SUYUNDA SOL SAHILDEDIR. 30°56'32" Doğu - 37°7'54" Kuzey**

YAĞIŞ ALANI : 238,60 km2 **YAKLAŞIK KOT :** 62 m

GÖZLEM SÜRESİ : 23.03.1964 - **30.09.2006**

ORTALAMA AKIMLAR : Gözlem süresinde 4.671 m3/sn. (19 Yıllık) 2006 Su yılında 3.056 m3/sn.

ANLIK EN ÇOK VE EN AZ AKIMLAR:

2006 Su yılında anlık ençok akım	:	**55.8**	**m3/sn**	**14.03.2006**
2006 Su yılında anlık enaz akım	:	**0.128**	**m3/sn**	**01.10.2005**
Gözlem süresinde anlık ençok akım	:	**517.**	**m3/sn**	**07.02.2003**
Gözlem süresinde anlık enaz akım	:	**0.064**	**m3/sn**	**13.10.2001**

Akımlar 01 Ekim 2005 'den 30 Eylül 2006' a kadar m3/sn olarak

Gün	Ekim	Kasım	Aralık	Ocak	şubat	Mart	Nisan	Mayıs	Haziran	Temmuz	Ağustos	Eylül
01	0.128	0.345	0.490	0.760	5.00	7.90	4.28	7.33	1.38	1.00	0.630	0.490
02	0.260	0.345	0.490	0.760	4.80	7.60	4.05	7.60	1.38	1.00	0.630	0.720
03	0.435	0.345	0.490	0.760	4.33	7.90	3.82	7.33	1.24	1.00	0.630	0.520
04	0.385	0.345	0.490	0.760	4.05	7.60	4.74	7.33	1.24	1.00	0.630	0.460
05	0.345	0.345	0.520	0.760	3.78	7.07	6.10	7.33	1.24	1.00	0.630	0.460
06	0.330	0.345	0.520	1.06	7.33	6.80	5.50	7.33	1.24	0.903	0.630	0.410
07	0.315	0.345	0.520	1.15	9.10	6.53	5.20	7.33	1.24	0.903	0.630	0.410
08	0.315	0.345	0.520	1.06	15.8	9.10	4.97	7.33	1.24	0.903	0.630	0.460
09	0.300	0.345	0.520	0.960	13.3	12.0	4.74	2.70	1.24	0.903	0.630	0.460
10	0.300	0.345	0.490	0.827	11.0	9.10	4.74	2.50	1.10	0.812	0.630	0.490
11	0.300	0.330	0.460	0.827	15.8	8.20	4.74	2.50	1.24	0.812	0.630	0.545
12	0.300	0.330	0.460	0.827	16.1	9.10	4.51	2.50	1.10	0.812	0.600	0.545
13	0.300	0.330	0.460	0.827	13.7	13.3	4.51	2.30	1.10	0.812	0.600	0.630
14	0.300	0.330	0.460	0.827	11.7	28.1	4.51	2.30	1.10	0.812	0.600	0.600
15	0.300	0.330	4.33	0.827	10.3	23.6	4.51	2.13	1.10	0.720	0.600	0.600
16	0.300	0.330	1.24	0.827	9.40	15.2	4.51	2.50	1.00	0.720	0.600	0.570
17	0.300	0.330	0.903	0.827	8.80	13.4	4.05	2.30	1.00	0.720	0.570	0.570
18	0.300	0.345	4.80	0.827	8.50	10.8	4.05	2.13	0.903	0.720	0.570	0.570
19	0.315	0.410	11.7	0.893	7.90	9.49	3.82	2.50	0.812	0.675	0.570	0.600
20	0.315	0.903	3.51	0.893	7.60	8.20	3.82	2.13	0.903	0.675	0.570	0.600
21	0.315	1.38	2.00	1.06	7.33	7.60	3.51	1.95	1.00	0.675	0.570	0.600
22	0.315	0.812	1.53	1.25	7.07	7.30	3.51	1.95	1.00	0.675	0.545	0.675
23	0.330	0.720	1.20	1.53	6.80	7.00	3.82	1.95	1.10	0.675	0.545	1.10
24	0.330	0.630	1.15	2.00	6.53	6.70	9.10	1.81	1.10	0.675	0.545	16.1
25	0.330	0.600	1.15	3.10	6.27	8.20	8.20	1.81	1.10	0.630	0.545	12.7
26	0.330	0.570	0.960	12.5	6.53	6.70	7.90	1.67	1.00	0.630	0.545	8.80
27	0.330	0.520	0.827	12.0	12.7	6.40	7.90	1.67	1.10	0.630	0.545	8.20
28	0.345	0.520	0.827	9.40	8.20	5.80	7.90	1.67	1.10	0.630	0.520	8.20
29	0.345	0.490	0.893	7.90	-----	5.20	7.90	1.53	1.24	0.675	0.520	8.20
30	0.345	0.490	0.827	7.07	-----	4.74	7.60	1.53	1.10	0.630	0.520	7.90
31	0.345	-----	0.760	6.00	-----	4.51	-----	1.53	-----	0.630	0.490	-----
Maks.	5.00	10.7	28.1	44.0	23.2	55.8	9.49	8.80	1.67	1.00	0.630	28.4
Min.	0.128	0.330	0.460	0.760	3.78	4.51	3.51	1.53	0.812	0.630	0.490	0.410
Ortalama	0.316	0.472	1.47	2.62	8.92	9.39	5.28	3.43	1.12	0.776	0.584	2.77
LT/SN/Km2	1.33	1.98	6.15	11.0	37.4	39.4	22.1	14.4	4.70	3.25	2.45	11.6
AKIM mm.	3.55	5.12	16.5	29.4	90.4	105.	57.4	38.6	12.2	8.71	6.55	30.1
MİL. M3	0.847	1.22	3.93	7.00	21.6	25.2	13.7	9.20	2.91	2.08	1.56	7.19

SU YILI (2006) YILLIK TOPLAM AKIM 96.44 MİLYON M3 404 MM. 12.8 LT/SN/Km2

09. Antalya Havzasi

D09A039 ONAÇ BRJ. GİRİŞ

YERİ : **BUCAK-BURDUR YOLUNUN 11.KM.SİNDEDİR.**
30°22'0" Doğu - 37°31'0" Kuzey

YAĞIŞ ALANI : 217,70 km2 **YAKLAŞIK KOT :** 835 m

GÖZLEM SÜRESİ : **18.11.1966 - 30.09.2006**

ORTALAMA AKIMLAR : Gözlem süresinde 0.663 m3/sn. (35 Yıllık) 2006 Su yılında 0.157 m3/sn.

ANLIK EN ÇOK VE EN AZ AKIMLAR:

2006 Su yılında anlık ençok akım	:	2.65	m3/sn	13.03.2006
2006 Su yılında anlık enaz akım	:	0.000	m3/sn	22.06.2006
Gözlem süresinde anlık ençok akım	:	378.	m3/sn	25.12.2001
Gözlem süresinde anlık enaz akım	:	0.000	m3/sn	24.07.1968

5. Anahtar Eğrisi (Seviyeler cm olarak)

Akımlar 01 Ekim 2005 'den 30 Eylül 2006' a kadar m3/sn olarak

Gün	Ekim	Kasım	Aralık	Ocak	Şubat	Mart	Nisan	Mayıs	Haziran	Temmuz	Ağustos	Eylül
01	0.024	0.010	0.039	0.039	0.096	0.046	1.06	0.352	0.017	KURU	KURU	0.010
02	0.024	0.010	0.039	0.039	0.063	0.046	0.660	0.352	0.017	KURU	KURU	0.010
03	0.024	0.010	0.039	0.039	0.063	0.046	0.537	0.352	0.010	KURU	KURU	0.010
04	0.024	0.010	0.039	0.039	0.063	0.046	0.537	0.352	0.008	KURU	KURU	0.010
05	0.024	0.024	0.039	0.039	0.063	0.046	0.475	0.290	0.007	KURU	0.002	0.010
06	0.024	0.032	0.039	0.032	0.063	0.046	0.475	0.290	0.005	KURU	0.002	0.010
07	0.024	0.063	0.039	0.024	0.046	0.046	0.475	0.290	0.004	KURU	0.002	0.010
08	0.024	0.063	0.039	0.017	0.046	0.130	0.475	0.210	0.002	0.005	0.007	0.010
09	0.024	0.039	0.039	0.010	0.046	0.475	0.475	0.210	KURU	0.007	0.007	0.010
10	0.024	0.039	0.039	0.010	0.130	0.352	0.413	0.170	KURU	0.010	0.007	KURU
11	0.024	0.039	0.039	0.010	0.210	0.250	0.413	0.170	KURU	0.008	0.010	KURU
12	0.024	0.039	0.039	0.080	0.413	0.250	0.413	0.170	KURU	0.007	0.010	KURU
13	0.024	0.039	0.039	0.080	0.250	2.65	0.413	0.170	KURU	0.005	0.010	KURU
14	0.024	0.039	0.039	0.080	0.170	2.15	0.475	0.210	KURU	KURU	0.010	KURU
15	0.024	0.039	0.039	0.080	0.130	2.15	0.537	0.210	KURU	KURU	0.010	KURU
16	0.024	0.039	0.039	0.080	0.113	1.55	0.598	0.210	KURU	KURU	0.010	KURU
17	0.024	0.039	0.039	0.080	0.096	1.45	0.537	0.210	KURU	KURU	0.010	KURU
18	0.024	0.039	0.039	0.080	0.096	1.35	0.475	0.210	KURU	KURU	0.010	KURU
19	0.024	0.039	0.039	0.063	0.113	1.35	0.475	0.170	KURU	KURU	0.010	KURU
20	0.017	0.039	0.039	0.063	0.080	1.25	0.475	0.170	KURU	KURU	0.010	KURU
21	0.017	0.039	0.039	0.046	0.080	1.16	0.475	0.130	KURU	KURU	0.010	KURU
22	0.017	0.039	0.039	0.046	0.063	1.16	0.413	0.130	KURU	KURU	0.010	KURU
23	0.017	0.039	0.039	0.046	0.063	1.06	0.537	0.113	KURU	KURU	0.010	KURU
24	0.017	0.039	0.039	0.250	0.046	1.06	0.537	0.113	KURU	KURU	0.010	KURU
25	0.010	0.039	0.039	0.413	0.046	1.06	0.413	0.096	KURU	KURU	0.010	KURU
26	0.010	0.039	0.039	0.598	0.039	1.06	0.352	0.096	KURU	KURU	0.010	KURU
27	0.010	0.039	0.039	0.475	0.039	1.06	0.290	0.063	KURU	KURU	0.010	KURU
28	0.010	0.039	0.039	0.250	0.046	1.06	0.290	0.039	KURU	KURU	0.010	KURU
29	0.010	0.039	0.039	0.250	-----	1.06	0.413	0.024	KURU	KURU	0.010	KURU
30	0.010	0.039	0.039	0.290	-----	0.957	0.352	0.024	KURU	KURU	0.010	KURU
31	0.010	-----	0.039	0.170	-----	1.06	-----	0.017	-----	KURU	0.010	-----
Maks.	0.024	0.063	0.039	0.598	0.413	2.65	1.06	0.352	0.017	0.010	0.010	0.010
Min.	0.010	0.010	0.039	0.010	0.039	0.046	0.290	0.017	KURU	KURU	KURU	KURU
Ortalama	0.020	0.036	0.039	0.123	0.099	0.885	0.482	0.181	0.002	0.001	0.008	0.003
LT/SN/Km2	0.091	0.165	0.179	0.566	0.455	4.07	2.21	0.832	0.011	0.006	0.035	0.014
AKIM mm.	0.242	0.429	0.480	1.52	1.10	10.9	5.74	2.23	0.028	0.017	0.094	0.036
MİL. M3	0.053	0.093	0.104	0.330	0.240	2.37	1.25	0.485	0.006	0.004	0.020	0.008

SU YILI (2006) YILLIK TOPLAM AKIM 4.96 MİLYON M3 23 MM. 0.7 LT/SN/Km2

09. Antalya Havzasi

D09A042 AĞLASUN Ç. AĞLASUN

YERİ : İSPARTA-AĞLASUN YOLUNA TAKİBEN AĞLASUNA VARILIR. AĞLASUN YOLUNUN ÇIKIŞ GÜZARGAHI ÜZERİNDEKİ AĞLASUN ÇAYININ 30 MT SOL SAHİLİNE TESİS EDİLMİŞTIR. HARİTA PAFTA NO: M25-D1 30°31'47" Doğu - 37°38'38" Kuzey

YAĞIŞ ALANI : 48,70 km2 YAKLAŞIK KOT : 1100 m

GÖZLEM SÜRESİ : 01.06.1990 - 30.09.2006

ORTALAMA AKIMLAR : Gözlem süresinde 0.531 m3/sn. (16 Yıllık) 2006 Su yılında 0.321 m3/sn.

ANLIK EN ÇOK VE EN AZ AKIMLAR:

2006 Su yılında anlık ençok akım	:	1.10	m3/sn	14.03.2006
2006 Su yılında anlık enaz akım	:	0.000	m3/sn	07.09.2006
Gözlem süresinde anlık ençok akım	:	15.0	m3/sn	24.12.1966
Gözlem süresinde anlık enaz akım	:	0.000	m3/sn	26.08.2001

2. Anahtar Eğrisi (Seviyeler cm olarak)

Seviye	Akım	Seviye	Akım	Seviye	Akım	Seviye	Akım
12	0.002	27	0.083	44	0.720	70	3.2
15	0.006	30	0.140	50	1.2	80	4.5
18	0.014	33	0.220	56	1.7	90	5.8
21	0.028	36	0.330	58	1.9	100	7.2
24	0.050	39	0.450	60	2.0		

Akımlar 01 Ekim 2005 'den 30 Eylül 2006' a kadar m3/sn olarak

Gün	Ekim	Kasım	Aralık	Ocak	Şubat	Mart	Nisan	Mayıs	Haziran	Temmuz	Ağustos	Eylül
01	0.188	0.404	0.404	0.404	0.440	0.404	0.578	0.440	0.188	0.188	0.140	0.100
02	0.164	0.404	0.404	0.404	0.404	0.404	0.578	0.440	0.188	0.188	0.140	0.100
03	0.164	0.404	0.404	0.404	0.404	0.404	0.532	0.486	0.188	0.188	0.120	0.100
04	0.164	0.404	0.404	0.404	0.404	0.404	0.532	0.440	0.188	0.188	0.120	0.120
05	0.164	0.404	0.404	0.404	0.404	0.404	0.532	0.440	0.188	0.188	0.120	0.120
06	0.188	0.404	0.404	0.404	0.404	0.404	0.532	0.404	0.164	0.164	0.120	0.120
07	0.212	0.404	0.404	0.404	0.404	0.404	0.486	0.404	0.164	0.164	0.100	KURU
08	0.236	0.368	0.404	0.404	0.486	0.404	0.486	0.404	0.164	0.164	0.100	KURU
09	0.296	0.368	0.404	0.404	0.486	0.404	0.440	0.404	0.164	0.164	0.100	KURU
10	0.296	0.368	0.404	0.368	0.578	0.440	0.440	0.404	0.164	0.164	0.100	KURU
11	0.368	0.368	0.404	0.368	0.532	0.440	0.440	0.404	0.164	0.140	0.100	KURU
12	0.368	0.368	0.404	0.368	0.532	0.404	0.440	0.404	0.164	0.140	0.100	KURU
13	0.404	0.368	0.404	0.368	0.486	0.440	0.440	0.404	0.164	0.140	0.100	KURU
14	0.368	0.404	0.404	0.332	0.578	1.10	0.440	0.404	0.164	0.140	0.100	KURU
15	0.368	0.404	0.404	0.332	0.532	1.03	0.440	0.404	0.164	0.140	0.100	KURU
16	0.368	0.404	0.404	0.332	0.486	0.988	0.440	0.404	0.164	0.140	0.100	KURU
17	0.404	0.404	0.404	0.332	0.486	0.950	0.440	0.404	0.164	0.140	0.100	KURU
18	0.486	0.404	0.404	0.368	0.486	0.762	0.440	0.368	0.164	0.140	0.100	KURU
19	0.486	0.404	0.404	0.368	0.440	0.716	0.440	0.404	0.164	0.140	0.100	KURU
20	0.486	0.404	0.404	0.404	0.440	0.670	0.440	0.404	0.164	0.140	0.100	KURU
21	0.532	0.404	0.404	0.404	0.440	0.624	0.440	0.404	0.188	0.140	0.100	KURU
22	0.532	0.404	0.404	0.404	0.440	0.578	0.440	0.404	0.188	0.140	0.100	KURU
23	0.486	0.404	0.404	0.404	0.404	0.578	0.440	0.368	0.188	0.140	0.100	KURU
24	0.404	0.404	0.404	0.440	0.404	0.532	0.440	0.296	0.188	0.140	0.100	KURU
25	0.368	0.404	0.404	0.532	0.404	0.532	0.440	0.236	0.188	0.140	0.100	KURU
26	0.368	0.404	0.404	0.532	0.404	0.486	0.440	0.212	0.188	0.140	0.100	KURU
27	0.404	0.404	0.404	0.532	0.404	0.486	0.440	0.188	0.188	0.140	0.100	KURU
28	0.404	0.404	0.404	0.440	0.404	0.486	0.440	0.188	0.188	0.140	0.100	KURU
29	0.404	0.404	0.404	0.440	-----	0.532	0.440	0.188	0.188	0.140	0.100	KURU
30	0.368	0.404	0.404	0.440	-----	0.532	0.440	0.188	0.188	0.140	0.100	KURU
31	0.368	-----	0.404	0.440	-----	0.532	-----	0.188	-----	0.140	0.100	-----
Maks.	0.532	0.404	0.404	0.532	0.578	1.10	0.578	0.486	0.188	0.188	0.140	0.120
Min.	0.164	0.368	0.404	0.332	0.404	0.404	0.440	0.188	0.164	0.140	0.100	KURU
Ortalama	0.349	0.397	0.404	0.406	0.454	0.564	0.465	0.359	0.176	0.152	0.105	0.022
LT/SN/Km2	7.16	8.15	8.30	8.34	9.33	11.6	9.54	7.37	3.61	3.11	2.16	0.452
AKIM mm.	19.2	21.1	22.2	22.3	22.6	31.0	24.7	19.7	9.37	8.34	5.78	1.17
MİL. M3	0.935	1.03	1.08	1.09	1.10	1.51	1.20	0.962	0.456	0.406	0.282	0.057

SU YILI (2006) YILLIK TOPLAM AKIM 10.11 MİLYON M3 208 MM. 6.6 LT/SN/Km2

09. Antalya Havzasi

D09A056 DÜDEN Ç. REG.ÇİKIS

YERİ : **ANTALYAYA 6.5 KM.MESAFEDEKİ DÜDEN REGÜLAÖRÜNDEDİR.**
30°45'21" Doğu - 36°56'19" Kuzey

YAĞIŞ ALANI : 1781,50 km2 **YAKLAŞIK KOT :** 96 m

GÖZLEM SÜRESİ : 01.05.1971 - **30.09.2006**

ORTALAMA AKIMLAR : **Gözlem** süresinde 14.678 m3/sn. (35 Yıllık) 2006 Su yılında 17.897 m3/sn.

ANLIK EN ÇOK VE EN AZ AKIMLAR:

2006 Su yılında anlık ençok akım	:	**72.0**	**m3/sn**	**14.03.2006**
2006 Su yılında anlık enaz akım	:	**2.22**	**m3/sn**	**20.09.2006**
Gözlem süresinde anlık ençok akım	:	**140.**	**m3/sn**	**27.05.1979**
Gözlem süresinde anlık enaz akım	:	**0.540**	**m3/sn**	**17.08.1979**

Akımlar 01 Ekim 2005 'den 30 Eylül 2006' a kadar m3/sn olarak

Gün	Ekim	Kasım	Aralık	Ocak	Şubat	Mart	Nisan	Mayıs	Haziran	Temmuz	Ağustos	Eylül
01	26.0	27.0	18.0	10.5	19.5	16.5	17.0	14.0	13.8	13.0	18.3	17.0
02	26.0	13.5	18.5	13.5	19.5	16.0	16.0	14.0	14.7	18.0	15.9	18.3
03	26.0	25.0	18.5	18.5	24.0	18.5	16.0	14.5	15.0	18.3	11.8	16.7
04	18.5	24.0	18.0	16.0	22.0	18.0	16.0	12.5	15.3	19.4	14.7	16.2
05	29.0	22.0	18.5	17.0	26.0	16.5	15.5	18.0	15.0	17.0	16.2	17.6
06	26.0	22.0	18.0	16.5	18.5	15.0	15.0	17.5	16.2	19.8	17.0	15.3
07	28.0	21.0	17.0	13.5	24.0	11.5	15.0	16.0	16.2	20.2	17.0	8.76
08	25.0	24.0	17.0	14.0	26.0	13.5	15.0	17.0	15.9	19.1	16.7	15.9
09	26.0	22.0	16.5	16.0	18.0	14.5	12.0	17.0	13.8	18.7	17.3	15.0
10	27.0	23.0	16.0	17.0	18.0	15.0	14.0	18.0	14.7	16.4	19.8	10.0
11	27.0	20.0	15.0	17.0	17.0	14.5	17.0	17.0	14.4	15.0	17.3	12.7
12	20.0	21.0	16.5	18.5	20.0	18.5	17.0	18.0	15.3	16.2	16.7	11.0
13	12.5	20.0	18.0	18.5	23.0	18.5	17.0	19.5	15.3	16.2	16.7	9.79
14	16.5	21.0	18.0	19.0	23.0	43.0	17.0	19.0	13.8	16.2	17.3	9.54
15	25.0	22.0	20.0	17.0	26.0	47.0	21.0	19.0	12.7	16.7	16.2	10.5
16	23.0	23.0	17.0	16.0	23.0	26.0	18.0	18.5	15.0	17.3	16.7	10.0
17	20.0	21.0	12.0	17.0	16.0	22.0	16.5	18.0	14.4	15.9	18.7	9.54
18	27.0	24.0	13.5	17.5	14.5	22.0	17.5	21.0	13.8	13.0	18.3	9.79
19	28.0	20.0	13.5	18.5	14.5	22.0	18.0	21.0	13.3	17.6	19.4	14.7
20	31.0	14.0	12.0	13.5	14.5	20.0	17.5	18.5	13.5	17.6	18.7	15.6
21	27.0	14.0	13.5	14.5	17.0	21.0	17.0	20.0	11.6	19.1	21.7	15.3
22	26.0	20.0	14.5	16.5	22.0	20.0	18.5	20.0	13.5	20.2	17.3	10.3
23	24.0	26.0	16.0	25.0	26.0	20.0	20.0	21.0	13.5	18.3	16.7	10.5
24	25.0	18.5	15.5	21.0	18.0	19.0	18.5	14.1	12.7	18.3	15.3	25.0
25	26.0	20.0	15.0	22.0	18.0	19.5	16.0	14.1	11.8	16.7	14.4	14.4
26	28.0	18.5	16.0	27.0	18.0	18.0	17.0	15.9	13.8	15.3	17.3	13.0
27	28.0	18.0	21.0	23.0	19.5	17.5	16.5	17.3	17.3	14.1	15.9	10.5
28	28.0	18.5	19.0	19.5	18.0	20.0	18.0	15.0	16.7	16.4	15.9	7.65
29	26.0	18.0	14.5	18.5	-----	17.5	17.0	15.0	11.3	16.7	15.9	13.0
30	25.0	18.0	11.5	19.0	-----	17.5	14.0	15.0	7.37	16.2	15.3	18.0
31	26.0	-----	10.5	20.0	-----	18.0	-----	15.0	-----	18.3	15.6	-----
Maks.	43.0	34.0	35.0	45.0	41.0	72.0	29.0	33.0	21.7	29.0	25.9	53.0
Min.	11.5	7.20	6.30	10.0	3.50	10.5	12.0	11.5	6.49	8.20	9.54	2.22
Ortalama	25.0	20.6	16.1	17.8	20.1	19.9	16.7	17.1	14.1	17.1	16.8	13.4
LT/SN/Km2	14.1	11.6	9.03	9.98	11.3	11.2	9.36	9.60	7.89	9.62	9.45	7.51
AKIM mm.	37.7	30.0	24.2	26.7	27.3	29.9	24.3	25.7	20.5	25.8	25.3	19.5
MİL. M3	67.1	53.5	43.1	47.6	48.7	53.3	43.2	45.8	36.4	45.9	45.1	34.7

SU YILI (2006) YILLIK TOPLAM AKIM 564.40 MİLYON M3 317 MM. 10.0 LT/SN/Km2

09. Antalya Havzasi

D09A057 HOYRAN D. GÖKÇEALİ

YERİ : SENİRKENT-YALVAÇ KARA YOLUNU TAKİBEN GÖKÇEALİ KÖYÜ YOLAYRIMINA VARILIR. KÖY YOLUNA SAPILARAK HOYRAN DERESİ KÖPRÜSÜNDEDİR.
30°56'0" Doğu - 38°17'0" Kuzey

YAĞIŞ ALANI : 185,00 km2 YAKLAŞIK KOT : 950 m

GÖZLEM SÜRESİ : 01.10.1996 - 30.09.2006

ORTALAMA AKIMLAR : Gözlem süresinde 0.287 m3/sn. (6 Yıllık) 2006 Su yılında 0.096 m3/sn.

ANLIK EN ÇOK VE EN AZ AKIMLAR:

2006 Su yılında anlık ençok akım	:	0.600	m3/sn	13.04.2006
2006 Su yılında anlık enaz akım	:	0.000	m3/sn	01.10.2005
Gözlem süresinde anlık ençok akım	:	10.5	m3/sn	12.10.1974
Gözlem süresinde anlık enaz akım	:	0.000	m3/sn	01.10.1972

2. Anahtar Eğrisi (Seviyeler cm olarak)

Seviye	Akım	Seviye	Akım	Seviye	Akım	Seviye	Akım
1	0.000	11	0.095	19	0.530	36	2.2
3	0.000	13	0.180	20	0.590	41	2.9
5	0.000	15	0.280	21	0.650	51	4.5
7	0.007	17	0.400	26	1.1	61	6.4
9	0.030	18	0.460	31	1.6	71	8.5

Akımlar 01 Ekim 2005 'den 30 Eylül 2006' a kadar m3/sn olarak

Gün	Ekim	Kasım	Aralık	Ocak	Şubat	Mart	Nisan	Mayıs	Haziran	Temmuz	Ağustos	Eylül
01	KURU	KURU	KURU	KURU	KURU	0.170	0.420	0.600	0.006	KURU	KURU	KURU
02	KURU	KURU	KURU	KURU	KURU	0.170	0.420	0.520	0.006	KURU	KURU	KURU
03	KURU	KURU	KURU	KURU	0.003	0.170	0.420	0.420	0.003	KURU	KURU	KURU
04	KURU	KURU	KURU	KURU	0.003	0.120	0.420	0.520	KURU	KURU	KURU	KURU
05	KURU	KURU	KURU	KURU	0.010	0.120	0.420	0.370	KURU	KURU	KURU	KURU
06	KURU	KURU	KURU	KURU	0.010	0.120	0.420	0.370	KURU	KURU	KURU	KURU
07	KURU	KURU	KURU	KURU	0.028	0.120	0.420	0.520	KURU	KURU	KURU	KURU
08	KURU	KURU	KURU	KURU	0.028	0.120	0.420	0.520	KURU	KURU	KURU	KURU
09	KURU	KURU	KURU	KURU	0.028	0.300	0.420	0.370	KURU	KURU	KURU	KURU
10	KURU	KURU	KURU	KURU	0.028	0.300	0.420	0.370	KURU	KURU	KURU	KURU
11	KURU	KURU	KURU	KURU	0.028	0.300	0.520	0.370	KURU	KURU	KURU	KURU
12	KURU	KURU	KURU	KURU	0.082	0.300	0.520	0.370	KURU	KURU	KURU	KURU
13	KURU	KURU	KURU	KURU	0.082	0.300	0.600	0.370	KURU	KURU	KURU	KURU
14	KURU	KURU	KURU	KURU	0.082	0.300	0.600	0.300	KURU	KURU	KURU	KURU
15	KURU	KURU	KURU	KURU	0.082	0.300	0.600	0.300	KURU	KURU	KURU	KURU
16	KURU	KURU	KURU	KURU	0.082	0.300	0.600	0.230	KURU	KURU	KURU	KURU
17	KURU	KURU	KURU	KURU	0.082	0.370	0.600	0.230	KURU	KURU	KURU	KURU
18	KURU	KURU	KURU	KURU	0.082	0.370	0.600	0.170	KURU	KURU	KURU	KURU
19	KURU	KURU	KURU	KURU	0.082	0.370	0.600	0.170	KURU	KURU	KURU	KURU
20	KURU	KURU	KURU	KURU	0.082	0.370	0.600	0.120	KURU	KURU	KURU	KURU
21	KURU	KURU	KURU	KURU	0.082	0.370	0.600	0.120	KURU	KURU	KURU	KURU
22	KURU	KURU	KURU	KURU	0.082	0.370	0.600	0.082	KURU	KURU	KURU	KURU
23	KURU	KURU	KURU	KURU	0.082	0.370	0.600	0.082	KURU	KURU	KURU	KURU
24	KURU	KURU	KURU	KURU	0.120	0.420	0.600	0.050	KURU	KURU	KURU	KURU
25	KURU	KURU	KURU	KURU	0.120	0.420	0.600	0.050	KURU	KURU	KURU	KURU
26	KURU	KURU	KURU	KURU	0.120	0.420	0.600	0.028	KURU	KURU	KURU	KURU
27	KURU	KURU	KURU	KURU	0.120	0.420	0.600	0.028	KURU	KURU	KURU	KURU
28	KURU	KURU	KURU	KURU	0.120	0.420	0.600	0.018	KURU	KURU	KURU	KURU
29	KURU	KURU	KURU	KURU	-----	0.420	0.600	0.018	KURU	KURU	KURU	KURU
30	KURU	KURU	KURU	KURU	-----	0.420	0.600	0.010	KURU	KURU	KURU	KURU
31	KURU	-----	KURU	KURU	-----	0.420	-----	0.010	-----	KURU	KURU	-----
Maks.	KURU	KURU	KURU	KURU	0.120	0.420	0.600	0.600	0.006	0.370	KURU	KURU
Min.	KURU	KURU	KURU	KURU	KURU	0.120	0.420	0.010	KURU	KURU	KURU	KURU
Ortalama	KURU	KURU	KURU	KURU	0.063	0.305	0.535	0.249	0.001	KURU	KURU	KURU
LT/SN/Km2	0.000	0.000	0.000	0.000	0.338	1.65	2.89	1.34	0.003	0.000	0.000	0.000
AKIM mm.	0.000	0.000	0.000	0.000	0.817	4.42	7.49	3.60	0.007	0.000	0.000	0.000
MİL. M3	0.000	0.000	0.000	0.000	0.151	0.817	1.39	0.666	0.001	0.000	0.000	0.000

SU YILI (2006) YILLIK TOPLAM AKIM 3.02 MİLYON M3 16 MM. 0.5 LT/SN/Km2

09. Antalya Havzasi

D09A060 ÇAYDERE EGİRDIR GÖL GİRİŞ

YERİ : EĞİRDİR-KONYA YOLUNU TAKİBEN 5 KM SONRA ÇAY DERE KÖPRÜSÜNE VARILARAK SAĞ TARAFA DOĞRU 300 MT GİDİLEREK ESKİ YOL ÜZERİNDEKİ KANALET YOLUNU TAKİBEN 1 KM SONRA İSTASYONA VARILIR.

HARİTA PAFTA NO: M25-B3

30°53'55" Doğu - 37°50'22" Kuzey

YAĞIŞ ALANI : 111,20 km2 YAKLAŞIK KOT : 935 m

GÖZLEM SÜRESİ : 01.10.1996 - 30.09.2006

ORTALAMA AKIMLAR : Gözlem süresinde 2.547 m3/sn. (9 Yıllık) 2006 Su yılında 1.798 m3/sn.

ANLIK EN ÇOK VE EN AZ AKIMLAR:

2006 Su yılında anlık ençok akım	:	12.9	m3/sn	14.03.2006
2006 Su yılında anlık enaz akım	:	0.000	m3/sn	01.10.2005
Gözlem süresinde anlık ençok akım	:	49.0	m3/sn	28.10.1978
Gözlem süresinde anlık enaz akım	:	0.000	m3/sn	01.10.1977

1. Anahtar Eğrisi (Seviyeler cm olarak)

Seviye	Akım	Seviye	Akım	Seviye	Akım	Seviye	Akım
1	0.000	16	0.130	31	1.0	141	39.5
4	0.000	19	0.230	61	7.1	151	44.0
7	0.010	22	0.360	91	17.5	161	48.5
10	0.029	25	0.520	121	30.5	171	53.0
13	0.065	28	0.740	131	35.0		

Akımlar 01 Ekim 2005 'den 30 Eylül 2006' a kadar m3/sn olarak

Gün	Ekim	Kasım	Aralık	Ocak	Şubat	Mart	Nisan	Mayıs	Haziran	Temmuz	Ağustos	Eylül
01	KURU	0.280	0.600	0.600	0.440	3.55	7.20	5.50	1.20	KURU	KURU	KURU
02	KURU	0.280	0.540	0.480	0.330	3.55	7.00	5.00	0.480	KURU	KURU	KURU
03	KURU	0.280	0.480	0.170	0.370	3.55	6.80	7.00	0.170	KURU	KURU	KURU
04	KURU	0.280	0.540	0.700	0.600	3.70	6.80	6.20	0.140	KURU	KURU	KURU
05	KURU	0.280	0.440	0.540	0.540	4.17	6.40	5.75	0.110	KURU	KURU	KURU
06	0.070	0.280	0.480	0.480	0.440	4.50	6.60	5.50	KURU	KURU	KURU	KURU
07	0.070	0.280	0.480	0.440	1.20	4.50	6.80	5.50	KURU	KURU	KURU	KURU
08	0.070	0.280	0.480	0.600	2.68	5.25	7.00	5.25	KURU	KURU	KURU	KURU
09	0.070	0.330	0.480	0.540	4.67	5.50	7.00	5.00	KURU	KURU	KURU	KURU
10	KURU	0.330	0.480	0.540	2.86	4.50	6.80	4.67	KURU	KURU	KURU	KURU
11	KURU	0.330	0.440	0.480	2.38	4.50	6.80	4.67	KURU	KURU	KURU	KURU
12	KURU	0.330	0.440	0.540	7.00	5.25	7.00	5.00	KURU	KURU	KURU	KURU
13	0.070	0.330	0.440	0.480	8.82	7.00	7.20	5.00	KURU	KURU	KURU	KURU
14	0.070	0.330	0.440	0.540	4.83	12.9	7.20	5.00	KURU	KURU	KURU	KURU
15	0.110	0.370	0.440	0.370	3.40	9.63	7.00	4.83	KURU	KURU	KURU	KURU
16	0.140	0.370	0.540	0.480	2.50	8.28	6.60	4.67	KURU	KURU	KURU	KURU
17	0.200	0.370	0.440	0.480	2.14	7.47	6.40	4.50	KURU	KURU	KURU	KURU
18	0.200	0.370	0.540	0.330	2.02	7.00	6.40	4.17	KURU	KURU	KURU	KURU
19	0.200	0.440	0.540	0.480	1.70	7.20	6.40	4.00	KURU	KURU	KURU	KURU
20	0.200	0.440	3.40	0.540	1.70	6.60	6.40	4.00	KURU	KURU	KURU	KURU
21	0.280	0.440	1.90	0.480	1.70	6.60	6.20	4.00	KURU	KURU	KURU	KURU
22	0.280	0.480	1.40	0.440	1.90	7.00	6.20	3.70	KURU	KURU	KURU	KURU
23	0.280	0.480	1.20	0.600	1.70	8.55	6.20	3.55	KURU	KURU	KURU	KURU
24	0.280	0.480	1.00	0.540	2.14	8.01	6.20	3.40	KURU	KURU	KURU	KURU
25	0.280	0.540	0.800	0.600	2.26	7.20	8.55	3.22	KURU	KURU	KURU	KURU
26	0.280	0.540	0.700	0.480	2.68	6.80	7.00	3.22	KURU	KURU	KURU	KURU
27	0.280	0.440	0.700	0.480	4.00	6.20	6.40	3.22	KURU	KURU	KURU	KURU
28	0.280	0.540	0.700	0.540	3.40	6.00	6.00	2.68	KURU	KURU	KURU	KURU
29	0.280	0.540	0.600	0.370	-----	7.00	5.75	2.26	KURU	KURU	KURU	KURU
30	0.280	0.440	0.600	0.540	-----	7.20	5.50	1.50	KURU	KURU	KURU	KURU
31	0.280	-----	0.600	0.540	-----	7.47	-----	1.20	-----	KURU	KURU	-----
Maks.	0.280	0.540	3.40	0.700	8.82	12.9	8.55	7.00	1.20	KURU	KURU	KURU
Min.	KURU	0.280	0.440	0.170	0.330	3.55	5.50	1.20	KURU	KURU	KURU	KURU
Ortalama	0.147	0.383	0.737	0.497	2.51	6.34	6.66	4.30	0.070	KURU	KURU	KURU
LT/SN/Km2	1.32	3.45	6.63	4.47	22.6	57.0	59.9	38.6	0.629	0.000	0.000	0.000
AKIM mm.	3.54	8.94	17.8	12.0	54.7	153.	155.	103.	1.63	0.000	0.000	0.000
MİL. M3	0.393	0.994	1.98	1.33	6.08	17.0	17.3	11.5	0.181	0.000	0.000	0.000

SU YILI (2006) YILLIK TOPLAM AKIM 56.76 MİLYON M3 510 MM. 16.2 LT/SN/Km2

09. Antalya Havzasi

D09A065 SÜCÜLLÜ BRJ. GİRİŞ

YERİ : YALVAÇ-SÜCÜLLÜ YOLUYLA BARAJA VARILIR. İSTASYON BARAJ-BAĞSARAY KÖYÜ YOLUNUN 1 KM SİNDE SOL TARAFTADIR.
31°8'0" Doğu - 38°25'0" Kuzey

YAĞIŞ ALANI : 103,48 km2 YAKLAŞIK KOT : 1198 m

GÖZLEM SÜRESİ : 01.10.1974 - 30.09.2006

ORTALAMA AKIMLAR : Gözlem süresinde 0.515 m3/sn. (31 Yıllık) 2006 Su yılında 0.403 m3/sn.

ANLIK EN ÇOK VE EN AZ AKIMLAR:

2006 Su yılında anlık ençok akım	:	3.62	m3/sn	29.04.2006
2006 Su yılında anlık enaz akım	:	0.025	m3/sn	07.07.2006
Gözlem süresinde anlık ençok akım	:	39.0	m3/sn	26.10.1978
Gözlem süresinde anlık enaz akım	:	0.000	m3/sn	02.07.1978

14. Anahtar Eğrisi (Seviyeler cm olarak)

Seviye	Akım	Seviye	Akım	Seviye	Akım	Seviye	Akım
5	0.002	13	0.100	30	1.3	80	11.0
7	0.008	14	0.140	40	2.5	90	14.0
9	0.023	15	0.180	50	4.0	100	17.5
11	0.054	20	0.460	60	6.0	110	20.5
12	0.076	25	0.800	70	8.0	120	24.0

Akımlar 01 Ekim 2005 'den 30 Eylül 2006' a kadar m3/sn olarak

Gün	Ekim	Kasım	Aralık	Ocak	Şubat	Mart	Nisan	Mayıs	Haziran	Temmuz	Ağustos	Eylül
01	0.042	0.071	0.140	0.100	0.140	0.736	1.56	2.51	0.192	0.100	0.025	0.025
02	0.042	0.071	0.140	0.100	0.140	0.736	1.56	2.32	0.140	0.071	0.025	0.025
03	0.042	0.071	0.140	0.100	0.140	0.652	1.56	3.06	0.140	0.071	0.025	0.025
04	0.042	0.071	0.140	0.071	0.140	0.652	1.56	2.14	0.140	0.100	0.025	0.025
05	0.042	0.071	0.140	0.071	0.140	0.652	1.56	1.82	0.100	0.071	0.025	0.042
06	0.042	0.100	0.140	0.071	0.140	0.652	1.69	0.820	0.100	0.042	0.025	0.042
07	0.042	0.100	0.140	0.071	0.192	0.652	1.69	0.736	0.100	0.025	0.025	0.042
08	0.042	0.100	0.140	0.071	0.192	0.652	1.69	0.652	0.100	0.025	0.025	0.042
09	0.042	0.140	0.140	0.071	0.192	0.736	1.69	0.652	0.100	0.025	0.025	0.042
10	0.042	0.140	0.140	0.071	0.192	0.820	1.43	0.400	0.244	0.025	0.025	0.025
11	0.042	0.140	0.140	0.071	0.192	0.916	1.30	0.568	0.192	0.025	0.025	0.025
12	0.042	0.140	0.140	0.071	0.192	1.01	1.30	0.652	0.140	0.025	0.025	0.025
13	0.042	0.140	0.140	0.071	0.192	1.11	1.20	0.652	0.140	0.025	0.025	0.025
14	0.042	0.140	0.140	0.071	0.244	1.30	1.43	0.652	0.140	0.025	0.025	0.025
15	0.042	0.140	0.140	0.071	0.244	1.30	1.69	0.568	0.140	0.025	0.025	0.025
16	0.042	0.140	0.140	0.071	0.244	1.30	1.69	0.568	0.140	0.025	0.025	0.025
17	0.042	0.140	0.140	0.071	0.296	1.30	2.14	0.568	0.140	0.025	0.025	0.025
18	0.042	0.140	0.140	0.071	0.296	1.20	2.69	0.568	0.100	0.025	0.025	0.025
19	0.042	0.140	0.140	0.140	0.296	1.11	2.69	0.568	0.100	0.025	0.025	0.025
20	0.042	0.140	0.140	0.140	0.348	1.11	2.69	0.568	0.100	0.025	0.025	0.025
21	0.042	0.140	0.140	0.140	0.348	1.01	3.06	0.484	0.140	0.025	0.025	0.025
22	0.042	0.140	0.140	0.140	0.348	0.916	3.25	0.484	0.140	0.025	0.025	0.042
23	0.042	0.140	0.140	0.140	0.348	1.01	1.82	0.400	0.071	0.025	0.025	0.042
24	0.042	0.140	0.140	0.140	0.348	1.01	1.30	0.348	0.042	0.025	0.025	0.042
25	0.042	0.140	0.140	0.140	0.348	1.01	2.69	0.296	0.042	0.025	0.025	0.042
26	0.042	0.140	0.140	0.140	0.348	1.20	3.06	0.244	0.042	0.025	0.025	0.042
27	0.071	0.140	0.100	0.140	0.400	1.43	3.25	0.192	0.042	0.025	0.025	0.042
28	0.071	0.140	0.100	0.140	0.484	1.56	3.43	0.192	0.192	0.025	0.025	0.042
29	0.071	0.140	0.100	0.140	-----	1.69	3.62	0.192	0.192	0.025	0.025	0.042
30	0.071	0.140	0.100	0.140	-----	1.69	3.62	0.192	0.192	0.025	0.025	0.042
31	0.071	-----	0.100	0.140	-----	1.69	-----	0.192	-----	0.025	0.025	-----
Maks.	0.071	0.140	0.140	0.140	0.484	1.69	3.62	3.06	0.244	0.100	0.025	0.042
Min.	0.042	0.071	0.100	0.071	0.140	0.652	1.20	0.192	0.042	0.025	0.025	0.025
Ortalama	0.047	0.125	0.134	0.103	0.254	1.06	2.13	0.783	0.126	0.035	0.025	0.033
LT/SN/Km2	0.451	1.20	1.29	0.993	2.46	10.2	20.6	7.56	1.22	0.337	0.242	0.318
AKIM mm.	1.21	3.12	3.46	2.66	5.95	27.4	53.4	20.3	3.16	0.902	0.647	0.825
MİL. M3	0.125	0.323	0.358	0.275	0.616	2.83	5.52	2.10	0.327	0.093	0.067	0.085

SU YILI (2006) YILLIK TOPLAM AKIM 12.72 MİLYON M3 123 MM. 3.9 LT/SN/Km2

09. Antalya Havzasi

D09A067 KARPUZ Ç. UZUNLAR

YERİ : **ALANYA-MANAVGAT YOLUNUN 17.KM.SİNDEN AYRILAN YOLUN 6 KM.SIN-DEKI UZUNLAR KÖYÜNÜN 5 KM.ILERISINDEDIR.**
31°37'22" Doğu - 36°44'38" Kuzey

YAĞIŞ ALANI : 303,20 km2 **YAKLAŞIK KOT :** 100 m

GÖZLEM SÜRESİ : **01.11.1976 - 30.09.2006**

ORTALAMA AKIMLAR : Gözlem süresinde 4.006 m3/sn. (29 Yıllık) 2006 Su yılında 3.311 m3/sn.

ANLIK EN ÇOK VE EN AZ AKIMLAR:

2006 Su yılında anlık ençok akım	:	**104.**	**m3/sn**	**12.02.2006**
2006 Su yılında anlık enaz akım	:	**0.004**	**m3/sn**	**01.10.2005**
Gözlem süresinde anlık ençok akım	:	**300.**	**m3/sn**	**15.11.1988**
Gözlem süresinde anlık enaz akım	:	**0.000**	**m3/sn**	**01.10.1999**

Akımlar 01 Ekim 2005 'den 30 Eylül 2006' a kadar m3/sn olarak

Gün	Ekim	Kasım	Aralık	Ocak	şubat	Mart	Nisan	Mayıs	Haziran	Temmuz	Ağustos	Eylül
01	0.005	0.044	0.054	0.160	3.90	4.20	7.10	1.35	0.160	0.088	0.039	0.024
02	0.006	0.054	0.054	0.120	3.30	3.70	7.10	1.20	0.160	0.064	0.039	0.024
03	0.010	0.064	0.054	0.120	2.60	3.50	6.90	1.20	0.160	0.054	0.039	0.019
04	0.034	0.520	0.054	0.105	2.00	3.30	6.60	1.10	0.140	0.054	0.039	0.019
05	0.039	0.120	0.054	0.088	1.75	3.00	6.00	0.960	0.120	0.054	0.039	0.019
06	0.039	0.088	0.054	0.076	24.0	2.80	5.40	0.960	0.105	0.088	0.039	0.019
07	0.044	0.076	0.054	0.088	42.0	2.80	5.20	0.800	0.105	0.105	0.039	0.019
08	0.044	0.064	0.054	0.120	46.9	4.90	5.20	0.800	0.105	0.064	0.039	0.019
09	0.044	0.064	0.054	0.105	32.0	17.5	5.20	0.640	0.088	0.054	0.039	0.019
10	0.044	0.064	0.044	0.088	27.0	9.60	4.60	0.580	0.088	0.054	0.034	0.019
11	0.044	0.064	0.044	0.088	39.0	7.10	4.40	0.520	0.088	0.044	0.034	0.019
12	0.054	0.064	0.044	0.076	54.8	6.30	4.40	0.460	0.088	0.044	0.034	0.019
13	0.044	0.064	0.044	0.064	41.0	8.10	4.20	0.400	0.088	0.044	0.034	0.019
14	0.044	0.064	0.044	0.054	30.0	21.0	3.90	0.320	0.088	0.044	0.034	0.019
15	0.044	0.064	0.044	0.044	23.0	27.0	3.90	0.320	0.076	0.044	0.034	0.019
16	0.088	0.064	0.054	0.044	19.5	19.0	5.20	0.290	0.076	0.039	0.034	0.019
17	0.064	0.064	0.054	0.044	16.5	14.5	4.90	0.250	0.076	0.039	0.034	0.019
18	0.054	0.120	4.20	0.044	13.5	13.0	4.40	0.230	0.076	0.039	0.034	0.019
19	0.054	0.290	36.0	0.044	11.5	21.0	3.70	0.230	0.064	0.039	0.034	0.019
20	0.054	3.70	17.0	31.0	9.60	14.0	3.50	0.230	0.064	0.039	0.028	0.019
21	0.044	1.45	7.10	7.20	8.40	12.0	3.30	0.230	0.064	0.039	0.028	0.019
22	0.044	0.460	3.90	4.20	7.10	10.5	3.00	0.200	0.064	0.039	0.024	0.019
23	0.044	0.230	2.40	4.20	6.60	9.80	2.60	0.200	0.064	0.039	0.024	0.019
24	0.044	0.160	1.45	5.40	6.00	9.60	2.40	0.180	0.064	0.039	0.019	0.019
25	0.044	0.120	0.880	45.0	5.40	9.80	2.20	0.180	0.054	0.039	0.019	0.160
26	0.044	0.088	0.640	29.0	4.90	10.5	1.90	0.180	0.054	0.039	0.024	0.039
27	0.044	0.076	0.460	17.0	4.90	10.0	1.75	0.180	0.054	0.039	0.024	0.015
28	0.044	0.054	0.320	11.5	4.90	9.10	1.75	0.160	0.054	0.039	0.024	0.013
29	0.044	0.054	0.250	8.40	-----	8.10	1.60	0.160	0.054	0.034	0.019	0.013
30	0.044	0.054	0.230	6.30	-----	7.80	1.45	0.160	0.105	0.034	0.019	0.007
31	0.044	-----	0.180	4.90	-----	7.20	-----	0.160	-----	0.034	0.019	-----
Maks.	0.200	14.5	65.7	68.6	104.	41.0	8.10	1.75	0.200	0.180	0.039	7.20
Min.	0.004	0.044	0.044	0.044	1.75	2.80	1.45	0.160	0.054	0.015	0.007	0.007
Ortalama	0.043	0.282	2.45	5.67	17.6	10.0	4.13	0.478	0.088	0.049	0.031	0.024
LT/SN/Km2	0.142	0.930	8.07	18.7	58.0	33.1	13.6	1.58	0.291	0.160	0.102	0.078
AKIM mm.	0.381	2.41	21.6	50.1	140.	88.5	35.3	4.23	0.754	0.430	0.274	0.203
MİL. M3	0.116	0.731	6.55	15.2	42.5	26.8	10.7	1.28	0.229	0.130	0.083	0.062

SU YILI (2006) YILLIK TOPLAM AKIM 104.38 MİLYON M3 344 MM. 10.9 LT/SN/Km2

09. Antalya Havzasi

D09A068 KARGI Ç. TÜRKLER

YERİ : **MANAVGAT ALANYA YOLUNUN 39 KM. SOLA ESKİ YOLA SAPILIR BU YOLU TAKIBEN 2 KM.SONRA TEKRAR SAĞA GIDEN YOLA DÖNÜLÜR 1 KM.ESKİ ALANYA YOLUNUN YIKIK KÖPRÜSÜNDE 50 M. MANSAPTADIR 01/10/1998 TARİHİNDE 1 KM MENBAA ALINMIŞTIR. 01.08.2008 TARİHİNDE EŞEL 43 CM AŞAĞI İNDİRİLDİ. 31°48'0" Doğu - 36°36'50" Kuzey**

YAĞIŞ ALANI : 336,32 km2 **YAKLAŞIK KOT :** 16 m

GÖZLEM SÜRESİ : 01.10.1976 - **30.09.2006**

ORTALAMA AKIMLAR : Gözlem süresinde 7.189 m3/sn. (20 Yıllık) 2006 Su yılında 3.631 m3/sn.

ANLIK EN ÇOK VE EN AZ AKIMLAR:

2006 Su yılında anlık ençok akım	:	**73.7**	**m3/sn**	**12.02.2006**
2006 Su yılında anlık enaz akım	:	**0.029**	**m3/sn**	**26.10.2005**
Gözlem süresinde anlık ençok akım	:	**602.**	**m3/sn**	**23.12.2001**
Gözlem süresinde anlık enaz akım	:	**0.012**	**m3/sn**	**09.09.2005**

Akımlar 01 Ekim 2005 'den 30 Eylül 2006' a kadar m3/sn olarak

Gün	Ekim	Kasım	Aralık	Ocak	Şubat	Mart	Nisan	Mayıs	Haziran	Temmuz	Ağustos	Eylül
01	0.048	0.075	0.300	1.40	4.91	5.24	7.08	2.96	1.33	0.620	0.430	0.175
02	0.075	0.930	0.300	1.33	4.74	4.91	7.08	3.09	1.40	0.620	0.430	0.175
03	0.075	0.570	0.300	1.27	4.24	4.74	6.85	2.96	1.33	0.620	0.430	0.175
04	0.075	0.350	0.240	1.27	3.75	4.57	7.08	2.70	1.27	0.620	0.430	0.175
05	0.075	0.350	0.240	1.27	3.90	4.57	6.62	2.58	1.27	0.620	0.430	0.175
06	0.075	0.300	0.240	1.27	4.91	4.40	5.93	2.58	1.20	0.620	0.370	0.175
07	0.075	0.240	0.240	1.40	40.1	4.07	5.70	2.47	1.20	0.620	0.370	0.175
08	0.075	0.240	0.195	1.51	42.6	4.74	5.47	2.47	1.13	0.620	0.315	0.175
09	0.075	0.195	0.195	1.40	35.2	13.3	5.24	2.70	1.13	0.580	0.315	0.175
10	0.075	0.150	0.195	1.40	26.3	8.84	5.07	2.70	1.13	0.580	0.315	0.175
11	0.108	0.150	0.195	1.27	35.2	7.08	5.07	2.70	1.05	0.580	0.315	0.175
12	0.108	0.108	0.150	1.27	49.5	6.39	5.07	2.70	1.05	0.580	0.315	0.100
13	0.075	0.075	0.150	1.27	45.0	9.17	5.07	2.70	0.970	0.580	0.315	0.100
14	0.075	0.048	0.150	1.27	27.3	15.5	5.07	2.58	0.970	0.580	0.315	0.100
15	0.075	0.048	0.300	1.20	18.9	23.4	5.07	2.35	0.890	0.580	0.315	0.100
16	0.075	0.048	0.400	1.13	14.8	17.3	6.16	2.27	0.890	0.580	0.315	0.100
17	0.048	0.029	0.350	1.13	12.2	14.0	6.16	2.19	0.820	0.580	0.315	0.100
18	0.048	0.705	1.50	1.13	10.5	12.6	5.47	2.11	0.820	0.580	0.315	0.100
19	0.048	1.80	31.3	2.27	9.17	18.0	4.91	2.11	0.820	0.580	0.315	0.100
20	0.048	2.29	16.6	11.5	8.19	15.8	4.74	2.03	0.820	0.580	0.315	0.100
21	0.048	1.60	7.31	7.54	7.54	13.7	4.74	2.03	0.820	0.490	0.240	0.100
22	0.048	1.12	4.74	4.91	7.08	11.9	4.57	1.95	0.760	0.490	0.240	0.100
23	0.048	1.02	3.60	4.91	6.62	10.8	4.24	1.95	0.760	0.490	0.240	0.175
24	0.048	0.855	3.09	5.93	6.39	10.5	4.24	1.84	0.760	0.490	0.240	0.240
25	0.048	0.705	2.96	34.7	6.16	13.7	3.90	1.84	0.760	0.490	0.240	0.240
26	0.029	0.630	2.83	30.3	5.93	11.2	3.60	1.73	0.760	0.490	0.240	0.175
27	0.029	0.570	2.83	15.5	5.70	10.1	3.21	1.73	0.690	0.490	0.240	0.175
28	0.029	0.510	2.70	9.50	5.47	9.17	3.34	1.62	0.690	0.430	0.240	0.175
29	0.029	0.455	2.27	7.08	-----	8.19	3.34	1.62	0.690	0.430	0.240	0.175
30	0.029	0.350	2.11	6.16	-----	7.54	3.21	1.51	0.580	0.430	0.240	0.175
31	0.029	-----	1.84	5.24	-----	7.31	-----	1.33	-----	0.430	0.240	-----
Maks.	0.195	2.83	40.6	62.5	73.7	27.8	14.0	3.21	1.40	0.620	0.430	0.240
Min.	0.029	0.029	0.150	1.05	3.60	3.75	3.21	1.33	0.580	0.430	0.240	0.100
Ortalama	0.060	0.551	2.90	5.44	16.2	10.1	5.11	2.26	0.959	0.551	0.310	0.152
LT/SN/Km2	0.177	1.64	8.62	16.2	48.0	30.0	15.2	6.72	2.85	1.64	0.923	0.451
AKIM mm.	0.474	4.24	23.1	43.3	116.	80.3	39.4	18.0	7.39	4.39	2.47	1.17
MİL. M3	0.159	1.43	7.76	14.6	39.1	27.0	13.2	6.06	2.48	1.47	0.832	0.394

SU YILI (2006) YILLIK TOPLAM AKIM 114.49 MİLYON M3 340 MM. 10.8 LT/SN/Km2

09. Antalya Havzasi

D09A075 GELENDOST D. AVŞAR KÖP.

YERİ : GELENDOST-AVŞAR KÖYÜ YOLUNDAKİ KÖPRÜNÜN 30 M.MENBAINDAIR.
30°59'26" Doğu - 38°7'53" Kuzey

YAĞIŞ ALANI : 988,96 km2 YAKLAŞIK KOT : 940 m

GÖZLEM SÜRESİ : 01.10.1976 - 30.09.2006

ORTALAMA AKIMLAR : Gözlem süresinde 1.756 m3/sn. (10 Yıllık) 2006 Su yılında 0.201 m3/sn.

ANLIK EN ÇOK VE EN AZ AKIMLAR:

2006 Su yılında anlık ençok akım	:	2.08	m3/sn	25.03.2006
2006 Su yılında anlık enaz akım	:	0.000	m3/sn	01.10.2005
Gözlem süresinde anlık ençok akım	:	51.0	m3/sn	26.10.1978
Gözlem süresinde anlık enaz akım	:	0.000	m3/sn	10.10.1977

3. Anahtar Eğrisi (Seviyeler cm olarak)

Seviye	Akım	Seviye	Akım	Seviye	Akım	Seviye	Akım
1	0.005	15	0.190	60	3.7	110	15.3
3	0.017	25	0.513	70	5.3	120	18.2
5	0.032	35	1.0	80	7.5	130	21.2
7	0.052	45	1.9	90	9.8	140	24.5
9	0.077	55	2.9	100	12.5	150	28.0

Akımlar 01 Ekim 2005 'den 30 Eylül 2006' a kadar m3/sn olarak

Gün	Ekim	Kasım	Aralık	Ocak	Şubat	Mart	Nisan	Mayıs	Haziran	Temmuz	Ağustos	Eylül
01	KURU	KURU	KURU	KURU	0.076	0.500	1.45	0.440	0.032	KURU	KURU	KURU
02	KURU	KURU	KURU	KURU	0.076	0.500	1.35	0.440	0.020	KURU	KURU	KURU
03	KURU	KURU	KURU	KURU	0.113	0.500	1.25	0.440	0.020	KURU	KURU	KURU
04	KURU	KURU	KURU	KURU	0.113	0.500	1.25	0.440	0.010	KURU	KURU	KURU
05	KURU	KURU	KURU	KURU	0.160	0.540	1.18	0.440	0.010	KURU	KURU	KURU
06	KURU	KURU	KURU	KURU	0.215	0.610	1.10	0.440	0.010	KURU	KURU	KURU
07	KURU	KURU	KURU	KURU	0.280	0.500	1.00	0.440	0.010	KURU	KURU	KURU
08	KURU	KURU	KURU	KURU	0.360	0.660	0.940	0.440	0.010	KURU	KURU	KURU
09	KURU	KURU	KURU	KURU	0.400	0.720	0.940	0.440	0.010	KURU	KURU	KURU
10	KURU	KURU	KURU	KURU	0.500	0.860	0.860	0.440	0.010	KURU	KURU	KURU
11	KURU	KURU	KURU	KURU	0.360	0.860	0.860	0.500	0.010	KURU	KURU	KURU
12	KURU	KURU	KURU	KURU	0.360	0.860	0.790	0.540	0.010	KURU	KURU	KURU
13	KURU	KURU	KURU	KURU	0.440	0.790	0.790	0.540	0.010	KURU	KURU	KURU
14	KURU	KURU	KURU	KURU	0.720	0.790	0.500	0.500	0.010	KURU	KURU	KURU
15	KURU	KURU	KURU	KURU	0.500	0.860	0.440	0.440	0.010	KURU	KURU	KURU
16	KURU	KURU	KURU	KURU	0.440	0.860	0.440	0.360	0.010	KURU	KURU	KURU
17	KURU	KURU	KURU	KURU	0.360	0.860	0.440	0.320	0.010	KURU	KURU	KURU
18	KURU	KURU	KURU	KURU	0.360	1.10	0.440	0.320	0.010	KURU	KURU	KURU
19	KURU	KURU	KURU	KURU	0.320	1.10	0.440	0.320	0.010	KURU	KURU	KURU
20	KURU	KURU	KURU	KURU	0.320	1.35	0.440	0.280	0.010	KURU	KURU	KURU
21	KURU	KURU	KURU	KURU	0.320	1.35	0.440	0.248	0.010	KURU	KURU	KURU
22	KURU	KURU	KURU	KURU	0.320	1.35	0.440	0.185	0.010	KURU	KURU	KURU
23	KURU	KURU	KURU	KURU	0.320	1.35	0.440	0.135	0.010	KURU	KURU	KURU
24	KURU	KURU	KURU	KURU	0.320	1.75	0.440	0.113	0.010	KURU	KURU	KURU
25	KURU	KURU	KURU	KURU	0.320	2.08	0.440	0.113	0.010	KURU	KURU	KURU
26	KURU	KURU	KURU	KURU	0.320	2.08	0.440	0.094	KURU	KURU	KURU	KURU
27	KURU	KURU	KURU	KURU	0.320	1.85	0.440	0.094	KURU	KURU	KURU	KURU
28	KURU	KURU	KURU	0.060	0.360	1.63	0.440	0.076	KURU	KURU	KURU	KURU
29	KURU	KURU	KURU	0.060	-----	1.45	0.440	0.060	KURU	KURU	KURU	KURU
30	KURU	KURU	KURU	0.060	-----	1.35	0.440	0.045	KURU	KURU	KURU	KURU
31	KURU	-----	KURU	0.060	-----	1.35	-----	0.032	-----	KURU	KURU	-----
Maks.	KURU	KURU	KURU	0.060	0.720	2.08	1.45	0.540	0.032	KURU	KURU	KURU
Min.	KURU	KURU	KURU	KURU	0.076	0.500	0.440	0.032	KURU	KURU	KURU	KURU
Ortalama	KURU	KURU	KURU	0.008	0.324	1.06	0.710	0.313	0.010	KURU	KURU	KURU
LT/SN/Km2	0.000	0.000	0.000	0.008	0.328	1.07	0.718	0.317	0.010	0.000	0.000	0.000
AKIM mm.	0.000	0.000	0.000	0.021	0.793	2.88	1.86	0.849	0.026	0.000	0.000	0.000
MİL. M3	0.000	0.000	0.000	0.021	0.784	2.84	1.84	0.839	0.025	0.000	0.000	0.000

SU YILI (2006) YILLIK TOPLAM AKIM 6.35 MİLYON M3 6 MM. 0.2 LT/SN/Km2

09. Antalya Havzasi

D09A084 OBA Ç. KADİPINARI

YERİ : OBA KÖYÜ YOLUNDAN DEĞİRMENDERE KÖYÜ YOLUNA SAPILIR.1.5 KM SONRA BU YOLU TAKIBEN ISTASYONA VARILIR. 23/08/2000 TARİHİNDEN 200 M MANSABA TAŞINMIŞTIR. 32°4'40" Doğu - 36°35'6" Kuzey

YAĞIŞ ALANI : 46,03 km2 **YAKLAŞIK KOT : 90 m**

GÖZLEM SÜRESİ : 19.08.1985 - 30.09.2006

ORTALAMA AKIMLAR : Gözlem süresinde 2.127 m3/sn. (19 Yıllık) 2006 Su yılında 1.249 m3/sn.

ANLIK EN ÇOK VE EN AZ AKIMLAR:

2006 Su yılında anlık ençok akım	:	27.7	m3/sn	08.02.2006
2006 Su yılında anlık enaz akım	:	0.019	m3/sn	03.04.2006
Gözlem süresinde anlık ençok akım	:	186.	m3/sn	15.12.1997
Gözlem süresinde anlık enaz akım	:	0.011	m3/sn	14.06.2001

Akımlar 01 Ekim 2005 'den 30 Eylül 2006' a kadar m3/sn olarak

Gün	Ekim	Kasım	Aralık	Ocak	Şubat	Mart	Nisan	Mayıs	Haziran	Temmuz	Ağustos	Eylül
01	0.223	0.254	0.284	0.500	1.60	1.60	0.500	1.07	0.438	0.377	0.284	0.254
02	0.223	0.254	0.284	0.500	1.50	1.60	0.500	1.07	0.438	0.377	0.315	0.254
03	0.223	0.254	0.284	0.500	1.33	1.50	0.500	1.07	0.438	0.377	0.315	0.254
04	0.223	0.254	0.284	0.500	1.27	1.50	0.469	1.07	0.408	0.377	0.284	0.254
05	0.223	0.254	0.284	0.469	1.20	1.40	0.469	1.07	0.438	0.377	0.284	0.284
06	0.223	0.254	0.284	0.438	1.20	1.40	0.469	1.07	0.408	0.408	0.315	0.284
07	0.223	0.254	0.284	0.438	7.88	1.40	0.469	1.00	0.408	0.377	0.315	0.284
08	0.192	0.254	0.254	0.377	20.0	1.50	0.469	1.00	0.408	0.377	0.284	0.284
09	0.192	0.254	0.254	0.438	20.3	2.85	0.469	1.00	0.408	0.408	0.315	0.284
10	0.223	0.254	0.284	0.408	13.8	3.45	0.750	0.875	0.408	0.377	0.284	0.284
11	0.254	0.223	0.284	0.408	19.3	3.00	1.00	0.750	0.438	0.346	0.284	0.284
12	0.254	0.223	0.284	0.408	22.6	2.70	1.50	0.750	0.438	0.408	0.284	0.284
13	0.254	0.254	0.284	0.408	23.3	3.60	1.40	0.625	0.408	0.377	0.284	0.284
14	0.254	0.254	0.254	0.408	17.0	3.00	1.40	0.625	0.408	0.346	0.315	0.284
15	0.223	0.254	0.254	0.408	11.3	2.55	1.33	0.625	0.408	0.346	0.284	0.254
16	0.254	0.223	0.254	0.408	7.44	2.10	1.33	0.500	0.377	0.346	0.284	0.254
17	0.254	0.254	0.254	0.408	5.81	1.90	1.33	0.625	0.377	0.346	0.315	0.254
18	0.254	0.284	0.625	0.408	4.88	1.60	1.33	0.500	0.377	0.346	0.284	0.254
19	0.223	0.284	9.66	0.750	4.32	1.27	1.33	0.500	0.408	0.346	0.284	0.254
20	0.254	0.377	8.76	2.70	3.45	0.875	1.27	0.500	0.408	0.346	0.284	0.284
21	0.223	0.346	3.90	3.30	2.55	0.625	1.27	0.469	0.377	0.315	0.284	0.254
22	0.223	0.315	1.50	1.60	2.30	0.625	1.27	0.500	0.408	0.315	0.284	0.254
23	0.223	0.315	1.13	1.33	2.20	0.625	1.20	0.469	0.377	0.346	0.284	0.254
24	0.254	0.315	1.07	1.60	2.10	0.500	1.20	0.500	0.377	0.346	0.284	0.284
25	0.254	0.284	1.00	7.44	1.90	0.500	1.20	0.469	0.377	0.315	0.254	0.284
26	0.254	0.254	0.750	14.3	1.90	0.500	1.13	0.500	0.408	0.346	0.284	0.254
27	0.254	0.284	0.750	7.88	1.80	0.500	1.07	0.469	0.408	0.315	0.254	0.254
28	0.254	0.284	0.625	4.60	1.70	0.500	1.13	0.469	0.408	0.315	0.254	0.254
29	0.254	0.284	0.500	3.00	-----	0.500	1.07	0.500	0.377	0.315	0.254	0.254
30	0.254	0.284	0.500	2.20	-----	0.500	1.07	0.469	0.377	0.315	0.254	0.254
31	0.254	-----	0.500	1.90	-----	0.500	-----	0.469	-----	0.315	0.284	-----
Maks.	1.20	0.625	14.1	16.2	27.7	5.30	1.60	1.70	1.70	2.00	2.00	1.80
Min.	0.169	0.192	0.192	0.158	1.20	0.020	0.019	0.181	0.158	0.158	0.146	0.158
Ortalama	0.237	0.271	1.16	1.95	7.35	1.51	0.996	0.696	0.405	0.353	0.286	0.267
LT/SN/Km2	5.15	5.89	25.2	42.4	160.	32.7	21.6	15.1	8.79	7.67	6.22	5.80
AKIM mm.	13.8	15.3	67.4	113.	387.	87.6	56.1	40.5	22.8	20.5	16.7	15.0
MİL. M3	0.635	0.703	3.10	5.22	17.8	4.03	2.58	1.86	1.05	0.945	0.766	0.692

SU YILI (2006) YILLIK TOPLAM AKIM 39.38 MİLYON M3 856 MM. 27.1 LT/SN/Km2

09. Antalya Havzasi

D09A086 AKSU D. BELENCE

YERİ : ISPSARTA-ŞÜTÇÜLER YOLUNDAN AYVALIYA VARILIR. AYVALIDAN AKSUÇAYINI TAKİBEN SOLDA BELENCE KÖYÜNDEDİR.
31°7'0" Doğu - 37°37'0" Kuzey

YAĞIŞ ALANI : 349,00 km2 YAKLAŞIK KOT : 1000 m

GÖZLEM SÜRESİ : 01.10.1986 - 30.09.2006

ORTALAMA AKIMLAR : Gözlem süresinde 4.519 m3/sn. (17 Yıllık) 2006 Su yılında 4.445 m3/sn.

ANLIK EN ÇOK VE EN AZ AKIMLAR:

2006 Su yılında anlık ençok akım	:	106.	m3/sn	13.02.2006
2006 Su yılında anlık enaz akım	:	0.066	m3/sn	01.10.2005
Gözlem süresinde anlık ençok akım	:	411.	m3/sn	24.02.1999
Gözlem süresinde anlık enaz akım	:	0.000	m3/sn	30.06.1991

5. Anahtar Eğrisi (Seviyeler cm olarak)

Akımlar 01 Ekim 2005 'den 30 Eylül 2006' a kadar m3/sn olarak

Gün	Ekim	Kasım	Aralık	Ocak	Şubat	Mart	Nisan	Mayıs	Haziran	Temmuz	Ağustos	Eylül
01	0.066	0.292	0.368	1.47	3.34	9.16	10.4	2.72	0.482	0.254	0.254	0.444
02	0.066	0.368	0.330	1.47	2.72	8.28	8.72	3.03	0.482	0.254	0.254	0.444
03	0.066	0.444	0.292	1.31	2.41	8.28	8.28	3.34	0.482	0.254	0.254	0.444
04	0.066	0.520	0.254	1.15	2.41	11.2	7.84	3.34	0.482	0.254	0.254	0.482
05	0.066	0.836	0.254	0.836	2.41	14.3	6.96	4.27	0.482	0.292	0.254	0.482
06	0.078	1.47	0.178	0.836	2.41	9.60	6.52	3.65	0.482	0.292	0.254	0.482
07	0.078	1.47	0.178	0.836	4.27	8.28	5.64	3.03	0.482	0.292	0.254	0.482
08	0.078	1.47	0.178	1.15	14.3	7.40	5.20	2.41	0.406	0.292	0.254	0.520
09	0.078	1.47	0.178	1.15	26.0	9.60	4.58	1.94	0.406	0.292	0.254	0.520
10	0.078	1.47	0.178	1.15	23.5	18.4	3.96	1.63	0.406	0.292	0.254	0.520
11	0.078	1.78	0.178	0.994	17.5	15.1	2.72	1.63	0.406	0.292	0.254	0.520
12	0.078	1.78	0.178	0.994	85.6	15.1	2.72	1.63	0.406	0.292	0.254	0.678
13	0.078	1.78	0.178	0.836	100.	28.4	2.72	1.63	0.406	0.292	0.254	0.678
14	0.078	1.78	0.178	0.836	47.8	28.4	2.72	1.63	0.406	0.292	0.254	0.678
15	0.091	2.10	0.178	0.678	24.3	80.4	2.72	1.63	0.406	0.292	0.254	0.678
16	0.091	2.10	0.216	0.520	14.3	63.2	2.72	1.63	0.406	0.292	0.254	0.836
17	0.091	2.10	0.178	0.520	14.3	53.4	2.72	1.47	0.406	0.292	0.254	0.836
18	0.103	2.72	0.216	0.520	6.96	54.8	2.72	1.31	0.406	0.292	0.406	0.836
19	0.103	2.72	0.444	0.520	5.64	52.0	2.72	1.15	0.406	0.292	0.444	0.836
20	0.103	2.72	12.8	0.520	5.64	52.0	2.72	0.994	0.406	0.292	0.444	0.994
21	0.103	3.34	11.2	3.03	6.52	25.2	2.72	0.994	0.406	0.292	0.482	0.994
22	0.103	1.94	8.72	2.72	7.40	24.3	2.72	0.994	0.330	0.254	0.482	0.994
23	0.115	3.34	4.89	1.94	7.40	25.2	2.72	0.836	0.330	0.254	0.482	0.994
24	0.115	1.94	3.34	3.34	6.96	24.3	2.72	0.520	0.330	0.254	0.482	1.15
25	0.140	1.31	2.41	5.64	6.52	26.0	2.72	0.520	0.330	0.254	0.444	1.15
26	0.140	0.836	1.94	4.89	5.64	24.3	2.72	0.482	0.292	0.254	0.444	1.31
27	0.216	0.368	1.47	4.58	5.20	20.1	1.94	0.482	0.292	0.254	0.444	1.31
28	0.216	0.482	1.15	4.58	5.20	16.7	1.94	0.482	0.292	0.254	0.444	1.15
29	0.216	0.444	0.994	3.96	-----	14.3	2.72	0.482	0.292	0.254	0.444	1.15
30	0.216	0.406	1.15	3.96	-----	12.8	3.03	0.482	0.292	0.254	0.444	0.994
31	0.216	-----	1.47	3.96	-----	12.8	-----	0.482	-----	0.254	0.444	-----
Maks.	0.216	3.34	12.8	5.64	106.	83.8	12.8	5.20	0.836	0.292	0.482	1.31
Min.	0.066	0.292	0.178	0.520	2.41	7.40	1.94	0.482	0.292	0.254	0.254	0.444
Ortalama	0.110	1.53	1.80	1.96	16.3	24.9	4.04	1.64	0.395	0.275	0.343	0.786
LT/SN/Km2	0.315	4.37	5.16	5.63	46.7	71.5	11.6	4.70	1.13	0.788	0.984	2.25
AKIM mm.	0.844	11.3	13.8	15.1	113.	191.	30.0	12.6	2.93	2.11	2.64	5.84
MİL. M3	0.295	3.96	4.83	5.26	39.5	66.8	10.5	4.39	1.02	0.736	0.920	2.04

SU YILI (2006) YILLIK TOPLAM AKIM 140.25 MİLYON M3 402 MM. 12.7 LT/SN/Km2

09. Antalya Havzasi

D09A088 DEGİRMENDERE D. SÜTÇÜLER

YERİ : ISPARTA-SÜTÇÜLER YOLUNDAN SÜTÇÜLERE VARILIR. 2 KM İLERSİNDEKİ YEŞİLDERE MAHALLESİNDEKİ KÖPRÜNÜN YANINDADIR.
31°0'0" Doğu - 41°50'0" Kuzey

YAĞIŞ ALANI : 130,90 km2 YAKLAŞIK KOT : 750 m

GÖZLEM SÜRESİ : 01.10.1986 - 30.09.2006

ORTALAMA AKIMLAR : Gözlem süresinde 1.489 m3/sn. (16 Yıllık) 2006 Su yılında 0.535 m3/sn.

ANLIK EN ÇOK VE EN AZ AKIMLAR:

2006 Su yılında anlık ençok akım	:	11.6	m3/sn	14.03.2006
2006 Su yılında anlık enaz akım	:	0.026	m3/sn	05.02.2006
Gözlem süresinde anlık ençok akım	:	224.	m3/sn	04.11.1995
Gözlem süresinde anlık enaz akım	:	0.000	m3/sn	05.09.1987

5. Anahtar Eğrisi (Seviyeler cm olarak)

Seviye	Akım	Seviye	Akım	Seviye	Akım	Seviye	Akım
13	0.012	23	0.125	33	0.600	70	9.6
15	0.020	25	0.190	35	0.800	90	18.5
17	0.034	27	0.260	37	1.0	110	29.0
19	0.055	29	0.340	39	1.2	120	35.0
21	0.082	31	0.460	50	3.3	350	175.

Akımlar 01 Ekim 2005 'den 30 Eylül 2006' a kadar m3/sn olarak

Gün	Ekim	Kasım	Aralık	Ocak	Şubat	Mart	Nisan	Mayıs	Haziran	Temmuz	Ağustos	Eylül
01	0.043	0.043	0.043	0.043	0.055	1.50	2.70	0.155	0.043	0.066	0.034	0.034
02	0.043	0.043	0.043	0.043	0.055	1.50	2.30	0.155	0.043	0.066	0.026	0.034
03	0.043	0.043	0.043	0.043	0.055	1.50	1.90	0.100	0.043	0.066	0.026	0.034
04	0.043	0.043	0.043	0.043	0.034	2.30	1.50	0.082	0.055	0.066	0.026	0.034
05	0.043	0.043	0.043	0.043	0.026	1.90	1.20	0.082	0.055	0.066	0.026	0.034
06	0.043	0.043	0.043	0.043	0.055	1.00	0.900	0.082	0.066	0.066	0.026	0.034
07	0.043	0.043	0.043	0.043	0.155	0.700	0.800	0.082	0.066	0.066	0.026	0.034
08	0.043	0.043	0.043	0.043	0.900	0.900	0.800	0.082	0.066	0.066	0.026	0.034
09	0.043	0.043	0.043	0.043	2.90	2.90	0.600	0.043	0.066	0.066	0.026	0.034
10	0.043	0.043	0.043	0.043	1.00	1.90	0.300	0.043	0.066	0.066	0.026	0.034
11	0.043	0.043	0.043	0.043	0.700	1.20	0.190	0.043	0.066	0.066	0.034	0.034
12	0.043	0.043	0.043	0.043	5.73	1.00	0.155	0.043	0.066	0.055	0.034	0.034
13	0.043	0.043	0.043	0.043	8.16	3.84	0.155	0.043	0.066	0.055	0.034	0.034
14	0.043	0.043	0.043	0.043	3.10	11.6	0.155	0.043	0.066	0.055	0.034	0.034
15	0.043	0.043	0.043	0.043	1.30	10.8	0.155	0.043	0.066	0.055	0.034	0.034
16	0.043	0.043	0.043	0.043	0.800	7.80	0.155	0.043	0.066	0.055	0.043	0.034
17	0.043	0.043	0.043	0.043	0.500	6.72	0.190	0.043	0.066	0.055	0.043	0.034
18	0.043	0.043	0.043	0.043	0.460	5.46	0.155	0.043	0.066	0.055	0.034	0.034
19	0.043	0.043	0.082	0.043	0.340	5.19	0.155	0.043	0.066	0.055	0.034	0.034
20	0.043	0.043	2.50	0.043	0.340	4.38	0.155	0.043	0.066	0.055	0.034	0.034
21	0.043	0.043	4.38	0.043	0.390	3.30	0.155	0.043	0.066	0.055	0.034	0.034
22	0.043	0.043	0.340	0.043	0.500	2.90	0.155	0.043	0.066	0.043	0.034	0.034
23	0.043	0.043	0.055	0.043	0.600	2.70	0.155	0.043	0.066	0.043	0.034	0.034
24	0.043	0.043	0.055	0.043	0.900	3.57	0.155	0.043	0.066	0.043	0.043	0.034
25	0.043	0.043	0.055	0.043	1.30	6.00	0.155	0.043	0.066	0.043	0.043	0.034
26	0.043	0.043	0.055	5.19	2.10	5.73	0.155	0.043	0.066	0.043	0.034	0.034
27	0.043	0.043	0.055	1.00	1.50	5.19	0.155	0.043	0.066	0.043	0.034	0.034
28	0.043	0.043	0.055	0.100	2.10	4.11	0.155	0.043	0.066	0.043	0.034	0.034
29	0.043	0.043	0.055	0.082	-----	3.57	0.155	0.043	0.066	0.043	0.034	0.034
30	0.043	0.043	0.043	0.055	-----	3.10	0.155	0.043	0.066	0.043	0.034	0.034
31	0.043	-----	0.043	0.055	-----	2.70	-----	0.043	-----	0.034	0.034	-----
Maks.	0.043	0.043	4.38	5.19	8.16	11.6	2.70	0.155	0.066	0.066	0.043	0.034
Min.	0.043	0.043	0.043	0.043	0.026	0.700	0.155	0.043	0.043	0.034	0.026	0.034
Ortalama	0.043	0.043	0.276	0.244	1.29	3.77	0.539	0.058	0.063	0.055	0.033	0.034
LT/SN/Km2	0.328	0.328	2.11	1.86	9.84	28.8	4.12	0.446	0.481	0.418	0.251	0.260
AKIM mm.	0.880	0.851	5.64	4.99	23.8	77.2	10.7	1.19	1.25	1.12	0.672	0.673
MİL. M3	0.115	0.111	0.738	0.653	3.12	10.1	1.40	0.156	0.163	0.147	0.088	0.088

SU YILI (2006) YILLIK TOPLAM AKIM 16.88 MİLYON M3 129 MM. 4.1 LT/SN/Km2

09. Antalya Havzasi

D09A089 DEGİRMENDERE SELİMLER

YERİ : ISPARTA - KOVADA - ÇANDIR YOLUNU TAKİBEN ORMAN DEPOSUNA ORADANDA AYNI YOLU TAKİBEN DEGİRMEN DERESİNE VARILIR. HARİTA PAFTA NO: N25-B2
30°54'30" Doğu - 37°27'50" Kuzey

YAĞIŞ ALANI : 313,90 km2 YAKLAŞIK KOT : 320 m

GÖZLEM SÜRESİ : 01.10.1986 - 30.09.2006

ORTALAMA AKIMLAR : Gözlem süresinde 6.540 m3/sn. (17 Yıllık) 2006 Su yılında 4.311 m3/sn.

ANLIK EN ÇOK VE EN AZ AKIMLAR:

2006 Su yılında anlık ençok akım	:	18.2	m3/sn	14.03.2006
2006 Su yılında anlık enaz akım	:	1.15	m3/sn	01.10.2005
Gözlem süresinde anlık ençok akım	:	180.	m3/sn	09.12.1998
Gözlem süresinde anlık enaz akım	:	0.000	m3/sn	01.03.1989

7. Anahtar Eğrisi (Seviyeler cm olarak)

Seviye	Akım	Seviye	Akım	Seviye	Akım	Seviye	Akım
10	0.880	60	9.4	210	81.0	260	118.
13	1.2	90	16.5	220	88.0	270	125.
16	1.6	120	28.5	230	96.0	280	132.
19	2.0	150	44.0	240	104.	290	141.
30	3.6	180	62.0	250	111.	300	150.

Akımlar 01 Ekim 2005 'den 30 Eylül 2006' a kadar m3/sn olarak

Gün	Ekim	Kasım	Aralık	Ocak	Şubat	Mart	Nisan	Mayıs	Haziran	Temmuz	Ağustos	Eylül
01	1.15	1.15	3.78	3.78	1.91	6.60	9.92	7.00	5.34	4.29	2.76	2.08
02	1.15	1.15	3.78	3.44	1.91	6.24	9.70	7.00	5.34	4.29	2.76	2.08
03	1.15	1.15	4.12	3.27	1.91	5.88	9.70	7.00	5.16	4.29	2.76	2.08
04	1.15	1.15	4.12	3.10	1.91	5.88	9.70	7.00	5.16	4.29	2.59	2.08
05	1.15	1.15	4.46	2.76	1.91	7.40	9.48	7.00	5.16	4.29	2.59	2.08
06	1.15	1.15	4.80	2.59	1.91	7.40	9.26	6.80	4.98	4.29	2.59	2.08
07	1.15	1.15	4.80	2.59	1.91	7.40	9.04	6.80	4.98	4.29	2.59	2.08
08	1.15	1.15	4.80	2.59	1.91	7.40	9.04	6.42	4.98	4.29	2.59	2.08
09	1.15	1.15	4.80	2.25	3.61	9.70	9.04	6.42	4.98	4.29	2.42	2.08
10	1.15	1.15	4.80	2.25	3.27	8.82	8.82	6.42	4.98	3.95	2.42	2.08
11	1.15	1.15	4.80	1.91	6.60	8.40	8.60	6.42	4.98	3.95	2.42	2.08
12	1.15	1.15	5.16	1.91	12.1	8.20	8.60	6.42	4.98	3.95	2.42	2.08
13	1.15	1.15	5.16	1.91	9.48	10.4	8.40	6.42	4.80	3.78	2.42	2.08
14	1.15	1.15	5.16	1.91	7.40	18.2	7.80	6.42	4.80	3.78	2.25	2.08
15	1.15	1.15	5.16	1.91	7.40	12.3	7.80	6.42	4.80	3.78	2.25	2.08
16	1.15	1.15	5.16	1.91	5.88	15.4	8.00	6.24	4.63	3.78	2.25	2.08
17	1.15	1.15	5.34	1.74	4.98	14.6	8.00	6.24	4.63	3.44	2.25	2.08
18	1.15	1.40	5.34	1.74	4.63	13.9	8.00	6.24	4.63	3.44	2.08	2.08
19	1.15	1.91	5.34	1.74	4.12	13.9	7.80	6.06	4.63	3.44	2.08	2.08
20	1.15	2.25	5.52	1.74	3.95	12.1	7.80	6.06	4.63	3.44	2.08	2.08
21	1.15	2.25	5.52	1.74	3.78	11.1	7.60	6.06	4.46	3.44	2.08	2.08
22	1.15	2.25	5.16	1.91	3.44	10.4	7.40	6.06	4.46	3.44	2.08	2.08
23	1.15	2.42	4.46	1.91	3.27	10.1	7.40	5.88	4.46	2.93	2.08	1.91
24	1.15	2.42	3.78	1.91	3.27	10.1	7.40	5.52	4.46	2.93	2.08	1.91
25	1.15	2.76	3.78	1.91	3.27	12.3	7.40	5.52	4.46	2.93	2.08	1.91
26	1.15	2.76	3.78	4.98	3.27	11.8	7.40	5.52	4.46	2.93	2.08	1.91
27	1.15	3.27	3.78	4.63	3.27	11.3	7.40	5.52	4.46	2.93	2.08	1.91
28	1.15	3.27	3.78	3.44	7.80	11.3	7.20	5.52	4.29	2.76	2.08	1.74
29	1.15	3.61	3.78	2.59	-----	10.6	7.20	5.34	4.29	2.76	2.08	1.74
30	1.15	3.78	3.78	2.25	-----	10.1	7.00	5.34	4.29	2.76	2.08	1.74
31	1.15	-----	3.78	1.91	-----	9.92	-----	5.34	-----	2.76	2.08	-----
Maks.	1.15	3.78	5.52	4.98	12.1	18.2	9.92	7.00	5.34	4.29	2.76	2.08
Min.	1.15	1.15	3.78	1.74	1.91	5.88	7.00	5.34	4.29	2.76	2.08	1.74
Ortalama	1.15	1.80	4.57	2.46	4.29	10.3	8.26	6.21	4.76	3.61	2.30	2.02
LT/SN/Km2	3.66	5.72	14.6	7.83	13.7	32.8	26.3	19.8	15.1	11.5	7.34	6.43
AKIM mm.	9.81	14.8	39.0	21.0	33.0	87.8	68.2	53.0	39.3	30.8	19.7	16.7
MİL. M3	3.08	4.66	12.2	6.59	10.4	27.6	21.4	16.6	12.3	9.67	6.17	5.23

SU YILI (2006) YILLIK TOPLAM AKIM 135.90 MİLYON M3 433 MM. 13.7 LT/SN/Km2

09. Antalya Havzasi

D09A091 TOPRAKSU MEVKİİ KIRKGÖZLER KANALI

YERİ : ANTALYA-ISPARTA YOLUNUN 26 KM. SİNDE VAKIFLAR KANALININ 1 KM. MEMBAĞINNDADIR.
30°34'50" Doğu - 37°4'19" Kuzey

YAĞIŞ ALANI : 2000,00 km2 YAKLAŞIK KOT : 300 m

GÖZLEM SÜRESİ : 06.12.1985 - 30.09.2006

ORTALAMA AKIMLAR : Gözlem süresinde 12.044 m3/sn. (21 Yıllık) 2006 Su yılında 11.703 m3/sn.

ANLIK EN ÇOK VE EN AZ AKIMLAR:

2006 Su yılında anlık ençok akım	:	21.7	m3/sn	24.03.2006
2006 Su yılında anlık enaz akım	:	2.74	m3/sn	10.09.2006
Gözlem süresinde anlık ençok akım	:	60.1	m3/sn	30.01.2004
Gözlem süresinde anlık enaz akım	:	0.000	m3/sn	25.10.1990

Akımlar 01 Ekim 2005 'den 30 Eylül 2006' a kadar m3/sn olarak

Gün	Ekim	Kasım	Aralık	Ocak	Şubat	Mart	Nisan	Mayıs	Haziran	Temmuz	Ağustos	Eylül
01	10.4	11.1	11.4	11.0	12.6	14.7	21.2	16.1	11.4	8.08	7.46	6.98
02	10.5	11.3	11.5	10.9	12.7	14.6	21.0	16.0	11.7	8.20	7.46	6.98
03	10.5	11.4	11.4	11.0	12.7	14.6	21.0	15.7	11.9	8.45	7.46	6.98
04	10.5	11.3	11.4	11.0	12.7	14.6	20.9	15.4	11.8	8.51	7.46	6.98
05	10.4	11.2	11.4	11.0	12.7	14.6	20.8	15.3	11.8	9.59	7.28	6.86
06	10.5	11.2	11.4	11.0	12.7	14.5	20.6	15.1	11.8	10.6	7.34	6.98
07	10.7	11.2	11.3	11.0	12.7	14.5	20.5	15.0	11.8	10.7	7.46	6.98
08	11.3	11.2	11.3	10.9	12.9	14.6	20.4	14.9	11.6	10.6	7.59	6.86
09	11.3	11.1	11.2	10.9	13.3	14.5	20.2	14.9	11.6	10.3	7.34	4.34
10	11.1	11.1	11.2	10.9	13.6	14.5	19.9	14.7	11.5	8.70	7.40	2.74
11	11.0	11.1	11.1	10.9	14.0	14.5	19.7	14.5	11.6	8.51	7.40	2.88
12	11.0	11.1	11.0	10.9	14.2	14.5	19.4	14.5	11.6	8.70	7.59	3.28
13	10.9	11.1	10.9	10.9	14.4	14.7	19.3	14.5	11.5	8.58	7.65	3.45
14	10.9	11.0	10.9	10.9	14.5	16.4	19.3	14.4	11.5	8.58	7.40	3.59
15	10.9	11.0	11.2	10.8	14.5	17.2	19.3	14.3	11.4	8.51	7.34	3.72
16	10.9	11.0	11.2	10.7	14.6	18.0	19.0	14.1	11.0	8.45	7.22	3.78
17	10.9	11.1	11.1	10.7	14.6	18.9	18.9	14.1	10.9	8.45	7.22	3.91
18	10.8	11.2	11.1	10.7	14.7	19.4	18.6	14.0	10.9	8.45	7.28	4.09
19	10.8	11.2	11.1	10.7	14.8	19.9	18.5	13.8	11.1	7.96	7.22	4.21
20	10.7	11.2	11.1	10.6	14.8	20.5	18.2	13.6	11.1	7.83	7.10	4.44
21	10.7	11.1	11.1	10.6	14.8	20.9	17.8	13.6	11.1	7.77	7.10	4.96
22	10.6	11.0	11.1	10.6	14.8	21.0	17.6	13.4	11.0	7.77	7.16	5.34
23	10.6	11.0	11.1	10.9	14.8	21.2	17.5	13.3	9.37	7.71	7.16	5.41
24	10.6	11.2	11.0	11.2	14.8	21.4	17.4	13.1	8.27	7.77	7.16	5.34
25	10.9	11.3	10.8	11.5	14.8	21.4	17.2	12.9	8.27	7.71	7.16	5.61
26	10.9	11.3	10.7	11.8	14.7	21.4	17.0	12.8	8.39	7.71	7.04	5.96
27	11.4	11.3	10.8	11.9	14.7	21.4	16.8	12.7	8.51	7.71	7.10	5.89
28	11.6	11.2	10.9	12.2	14.7	21.4	16.7	12.4	8.58	7.71	7.22	5.41
29	11.0	11.3	10.9	12.3	-----	21.4	16.5	12.4	9.15	7.59	7.16	4.57
30	10.4	11.2	10.9	12.4	-----	21.3	16.3	12.3	9.48	7.52	7.10	4.40
31	10.7	-----	10.9	12.6	-----	21.2	-----	11.6	-----	7.59	7.04	-----
Maks.	11.8	11.5	11.6	12.7	15.0	21.7	21.6	16.5	12.1	10.9	8.20	7.16
Min.	10.3	10.9	10.6	10.5	12.6	14.4	16.1	11.6	8.20	7.40	6.92	2.74
Ortalama	10.8	11.2	11.1	11.1	14.0	17.9	18.9	14.0	10.7	8.46	7.29	5.10
LT/SN/Km2	5.41	5.58	5.55	5.57	7.00	8.93	9.46	7.02	5.36	4.23	3.65	2.55
AKIM mm.	14.5	14.5	14.9	14.9	16.9	23.9	24.5	18.8	13.9	11.3	9.77	6.61
MİL. M3	29.0	28.9	29.8	29.8	33.9	47.8	49.0	37.6	27.8	22.7	19.5	13.2

SU YILI (2006) YILLIK TOPLAM AKIM 369.00 MİLYON M3 184 MM. 5.9 LT/SN/Km2

09. Antalya Havzasi

D09A095 ÇANDIR ÇAYI YEMİŞLİ PINAR MEVKİİ

YERİ : ANTALYA NIN 15.KM.BATISINDA BULUNAN ÇAKIRLAR NAHİYESİ MERKEZİNE GİDİLİR. BURADAN BATIYA DOGRU 11. KM. GİDİLİNCE ISTASYONA VARILIR.RÖPER: SAĞ SAHİLDE TELEFERİK BETONU ÜZERİNDEKİ ÇELİK HALATIN GEÇTİĞİ DEMİRDİR. İSTASYON 3 M. EŞELLİ VE LIMNIGRAFLIDIR
31°28'2" Doğu - 36°49'30" Kuzey

YAĞIŞ ALANI : 164,00 km2 YAKLAŞIK KOT : 160 m

GÖZLEM SÜRESİ : 01.10.1989 - 30.09.2006

ORTALAMA AKIMLAR : Gözlem süresinde 1.371 m3/sn. (13 Yıllık) 2006 Su yılında 1.236 m3/sn.

ANLIK EN ÇOK VE EN AZ AKIMLAR:

2006 Su yılında anlık ençok akım	:	121.	m3/sn	13.03.2006
2006 Su yılında anlık enaz akım	:	0.150	m3/sn	31.08.2006
Gözlem süresinde anlık ençok akım	:	282.	m3/sn	25.12.2003
Gözlem süresinde anlık enaz akım	:	0.010	m3/sn	01.10.1989

Akımlar 01 Ekim 2005 'den 30 Eylül 2006' a kadar m3/sn olarak

Gün	Ekim	Kasım	Aralık	Ocak	Şubat	Mart	Nisan	Mayıs	Haziran	Temmuz	Ağustos	Eylül
01	0.350	0.518	0.518	0.695	1.49	1.49	2.30	1.70	0.830	0.690	0.260	0.220
02	0.462	0.518	0.518	0.630	1.49	1.49	2.23	2.00	0.975	0.760	0.380	0.380
03	0.518	0.574	0.518	0.630	1.40	1.49	2.15	2.00	0.975	0.760	0.380	0.380
04	0.462	0.760	0.462	0.630	1.30	1.49	2.08	2.00	0.975	0.760	0.380	0.320
05	0.462	0.630	0.462	0.574	1.30	1.49	2.00	2.00	0.975	0.760	0.380	0.320
06	0.406	0.630	0.462	0.630	1.75	1.40	2.00	2.00	0.975	0.760	0.380	0.320
07	0.406	0.630	0.462	0.630	2.80	0.975	2.00	2.00	0.975	0.690	0.440	0.320
08	0.406	0.630	0.462	0.630	5.03	1.05	2.00	1.85	0.975	0.620	0.380	0.320
09	0.406	0.630	0.462	0.574	3.71	1.13	2.00	1.85	0.975	0.620	0.380	0.260
10	0.406	0.574	0.462	0.574	3.10	1.05	2.00	1.70	0.975	0.560	0.380	0.260
11	0.406	0.518	0.462	0.574	3.71	0.975	1.70	1.63	0.975	0.560	0.380	0.260
12	0.518	0.518	0.462	0.574	2.90	2.23	1.70	1.63	0.975	0.560	0.380	0.260
13	0.518	0.518	0.462	0.574	2.51	33.0	1.85	1.63	0.975	0.500	0.380	0.260
14	0.518	0.518	0.462	0.574	2.23	17.0	1.85	1.55	0.900	0.500	0.380	0.260
15	0.518	0.518	0.462	0.518	2.04	6.40	2.90	1.55	0.900	0.500	0.380	0.260
16	0.518	0.518	0.462	0.518	1.85	4.80	8.10	1.55	0.900	0.500	0.380	0.260
17	0.518	0.518	0.462	0.518	1.75	4.04	2.80	1.55	0.900	0.500	0.380	0.260
18	0.574	0.833	0.462	0.518	1.66	3.66	2.80	1.55	0.900	0.500	0.320	0.260
19	0.574	0.760	1.30	0.518	1.66	3.66	2.60	1.48	0.830	0.500	0.320	0.260
20	0.574	1.20	0.980	0.518	1.58	3.47	2.50	1.48	0.830	0.500	0.320	0.260
21	0.574	0.695	0.630	0.518	1.58	2.60	2.40	1.40	0.830	0.440	0.320	0.260
22	0.518	0.630	0.630	0.518	1.58	2.90	2.30	1.30	0.830	0.440	0.320	0.320
23	0.518	0.630	0.574	4.80	1.49	2.80	2.40	1.20	0.760	0.440	0.320	0.320
24	0.518	0.630	0.574	7.40	1.49	2.70	2.40	1.20	0.760	0.440	0.320	0.320
25	0.518	0.574	0.574	4.40	1.49	2.60	2.30	1.13	0.760	0.440	0.260	0.320
26	0.462	0.574	0.518	2.51	1.49	2.60	2.15	1.05	0.760	0.440	0.260	0.320
27	0.406	0.574	0.518	2.04	1.49	2.90	2.15	1.05	0.760	0.440	0.220	0.320
28	0.406	0.574	1.94	1.85	1.49	2.70	2.15	1.05	0.760	0.440	0.220	0.320
29	0.462	0.574	1.13	1.66	-----	2.50	2.08	0.975	0.975	0.380	0.220	0.320
30	0.462	0.574	0.833	1.58	-----	2.40	1.48	0.975	0.620	0.380	0.220	0.180
31	0.300	-----	0.760	1.49	-----	1.85	-----	0.690	-----	0.220	0.150	-----
Maks.	0.574	2.32	6.40	17.0	10.1	121.	66.0	2.08	3.28	0.830	0.440	0.380
Min.	0.300	0.518	0.462	0.518	1.30	0.975	1.48	0.690	0.620	0.220	0.150	0.180
Ortalama	0.473	0.618	0.627	1.30	2.05	3.90	2.38	1.51	0.884	0.535	0.329	0.290
LT/SN/Km2	2.88	3.77	3.82	7.94	12.5	23.8	14.5	9.19	5.39	3.27	2.00	1.77
AKIM mm.	7.73	9.77	10.2	21.3	30.2	63.7	37.6	24.6	14.0	8.75	5.37	4.58
MİL. M3	1.27	1.60	1.68	3.49	4.96	10.4	6.17	4.04	2.29	1.43	0.880	0.752

SU YILI (2006) YILLIK TOPLAM AKIM 38.96 MİLYON M3 238 MM. 7.5 LT/SN/Km2

09. Antalya Havzasi

D09A100 BAŞAK D. YANIKKÖY

YERİ : ISPARTA-AKSU KAZASINA VE ORADAN AKSU KOÇULAR VE KARACAHİSARŞOSE YOLUYLA KARACAHİSAR IN YANIKKÖY MAHALLESİNE VARILIR. İSTASYON KÖYÜN ALTINDAKİ KÖPRÜNÜN SOL SAHİLE TESİS EDİLMİŞTİR. 31°9'0" Doğu - 37°39'0" Kuzey

YAĞIŞ ALANI : 223,00 km2 YAKLAŞIK KOT : 1085 m

GÖZLEM SÜRESİ : 14.08.1990 - 30.09.2006

ORTALAMA AKIMLAR : Gözlem süresinde 3.575 m3/sn. (16 Yıllık) 2006 Su yılında 3.206 m3/sn.

ANLIK EN ÇOK VE EN AZ AKIMLAR:

2006 Su yılında anlık ençok akım	:	12.5	m3/sn	14.03.2006
2006 Su yılında anlık enaz akım	:	0.000	m3/sn	29.09.2006
Gözlem süresinde anlık ençok akım	:	175.	m3/sn	05.11.1995
Gözlem süresinde anlık enaz akım	:	0.000	m3/sn	01.10.1991

2. Anahtar Eğrisi (Seviyeler cm olarak)

Seviye	Akım	Seviye	Akım	Seviye	Akım	Seviye	Akım
10	0.200	70	7.0	180	54.0	250	100.
20	0.680	90	12.0	200	66.0	260	110.
30	1.3	120	23.0	220	80.0	270	120.
40	2.3	140	31.0	230	88.0	300	140.
50	3.6	160	44.0	240	92.0	400	225.

Akımlar 01 Ekim 2005 'den 30 Eylül 2006' a kadar m3/sn olarak

Gün	Ekim	Kasım	Aralık	Ocak	Şubat	Mart	Nisan	Mayıs	Haziran	Temmuz	Ağustos	Eylül
01	7.20	0.540	0.340	0.620	5.00	12.1	5.60	3.88	4.44	4.44	1.30	0.680
02	6.40	0.440	0.340	0.620	5.00	12.1	5.00	3.60	4.44	4.16	1.30	0.680
03	5.40	0.440	0.400	0.620	5.55	8.60	5.20	4.86	4.30	3.88	1.23	0.680
04	4.70	0.440	0.400	0.620	5.55	7.90	4.86	4.30	4.16	3.60	1.23	0.680
05	2.90	0.440	0.400	0.620	6.40	7.30	4.72	4.16	4.16	3.33	1.23	0.680
06	1.90	0.440	0.400	0.620	7.40	10.0	4.58	4.30	4.16	3.07	1.23	0.680
07	1.10	0.440	0.400	0.620	7.40	9.00	4.44	4.72	4.16	3.07	1.23	0.680
08	0.680	0.440	0.440	0.760	7.40	7.90	4.30	4.58	4.16	2.93	1.23	0.680
09	0.620	0.440	0.440	0.760	7.40	7.30	4.30	4.58	4.16	2.80	1.23	0.680
10	0.620	0.440	0.440	0.920	7.90	7.20	4.16	4.44	4.02	2.68	1.23	0.680
11	0.620	0.440	0.440	1.10	7.90	9.00	4.02	4.44	4.02	2.55	1.23	0.680
12	0.620	0.440	0.440	1.10	8.40	8.15	4.44	4.30	4.02	2.55	1.23	0.680
13	0.620	0.440	0.440	1.10	8.40	7.30	4.44	4.30	4.02	2.43	1.17	0.680
14	0.620	0.440	0.440	1.55	8.80	12.5	4.86	4.30	4.30	2.30	1.17	0.680
15	0.540	0.440	0.440	1.55	8.80	12.5	5.00	4.30	4.44	2.30	1.17	0.680
16	0.540	0.400	0.440	1.76	9.20	12.5	5.00	4.30	4.44	2.20	1.17	0.680
17	0.540	0.400	0.440	1.76	9.20	12.3	4.86	4.30	4.44	2.20	1.03	0.680
18	0.540	0.340	0.440	1.76	9.70	8.60	4.58	4.30	4.44	2.10	1.03	0.680
19	0.540	0.340	0.440	2.10	9.70	10.2	4.44	4.02	4.30	2.10	1.03	0.680
20	0.540	0.340	0.440	2.10	10.3	7.00	4.44	4.02	4.30	2.00	1.03	0.680
21	0.540	0.340	0.440	2.10	10.3	7.00	4.44	4.02	4.16	2.00	0.967	0.680
22	0.540	0.340	0.440	2.30	10.3	7.00	4.44	4.16	4.16	2.00	0.967	0.680
23	0.540	0.340	0.440	2.30	10.8	6.20	4.30	4.16	4.16	1.90	0.967	0.680
24	0.540	0.340	0.440	2.30	10.8	7.20	6.00	4.30	4.16	1.90	0.967	0.680
25	0.540	0.340	0.540	2.90	11.1	8.20	4.86	4.44	4.16	1.80	0.900	3.05
26	0.540	0.340	0.540	3.30	11.1	7.20	4.44	4.44	4.44	1.80	0.845	2.50
27	0.540	0.340	0.540	3.30	12.1	6.00	4.44	4.44	4.44	1.60	0.790	2.30
28	0.540	0.340	0.540	3.55	12.1	5.40	4.16	4.44	4.44	1.60	0.790	2.30
29	0.540	0.340	0.620	3.70	-----	5.40	4.02	4.44	4.44	1.60	0.735	2.30
30	0.540	0.340	0.620	4.20	-----	5.20	4.02	4.30	4.44	1.50	0.735	2.10
31	0.540	-----	0.620	4.70	-----	6.00	-----	4.44	-----	1.30	0.680	-----
Maks.	7.20	0.540	0.620	4.70	12.1	12.5	6.00	4.86	4.44	4.44	1.30	3.05
Min.	0.540	0.340	0.340	0.620	5.00	5.20	4.02	3.60	4.02	1.30	0.680	KURU
Ortalama	1.39	0.397	0.457	1.85	8.71	8.40	4.61	4.31	4.26	2.44	1.07	1.03
LT/SN/Km2	6.25	1.78	2.05	8.29	39.1	37.6	20.7	19.3	19.1	10.9	4.78	4.61
AKIM mm.	16.7	4.62	5.49	22.2	94.5	101.	53.6	51.8	49.5	29.3	12.8	12.0
MİL. M3	3.73	1.03	1.23	4.95	21.1	22.5	12.0	11.5	11.0	6.54	2.85	2.67

SU YILI (2006) YILLIK TOPLAM AKIM 101.10 MİLYON M3 453 MM. 14.4 LT/SN/Km2

09. Antalya Havzasi

D09A101 KÖPRÜÇAY KARAKAYA

YERİ : SERİK MANAVGAT KARAYOLUNDAN AŞPENDOS HARABELERINE SAPILIR. TAKRIBEN 8 KM.SONRA REĞÜLATÖRE ULAŞILIR. BURADAN 2 KM.SONRA İSTASYONA VARILIR.
31°11'57" Doğu - 36°58'49" Kuzey

YAĞIŞ ALANI : 2330,00 km2 YAKLAŞIK KOT : 20 m

GÖZLEM SÜRESİ : 01.10.1991 - 30.09.2006

ORTALAMA AKIMLAR : Gözlem süresinde 95.196 m3/sn. (9 Yıllık) 2006 Su yılında 79.643 m3/sn.

ANLIK EN ÇOK VE EN AZ AKIMLAR:

2006 Su yılında anlık ençok akım	:	685.	m3/sn	11.02.2006
2006 Su yılında anlık enaz akım	:	30.2	m3/sn	14.10.2005
Gözlem süresinde anlık ençok akım	:	2318	m3/sn	25.11.2001
Gözlem süresinde anlık enaz akım	:	10.8	m3/sn	31.10.1994

Akımlar 01 Ekim 2005 'den 30 Eylül 2006' a kadar m3/sn olarak

Gün	Ekim	Kasım	Aralık	Ocak	Şubat	Mart	Nisan	Mayıs	Haziran	Temmuz	Ağustos	Eylül
01	32.6	31.0	69.4	57.2	89.5	147.	145.	90.7	64.1	42.6	34.2	44.1
02	32.6	31.0	64.8	57.2	86.9	142.	140.	99.8	61.6	41.7	34.2	44.1
03	36.0	31.8	64.8	57.2	83.1	142.	136.	96.7	61.6	42.6	35.0	48.0
04	36.0	58.7	64.8	57.2	81.9	153.	133.	93.6	61.6	42.6	34.2	49.9
05	34.2	61.8	63.3	57.2	80.6	143.	131.	92.0	61.6	44.5	34.2	46.1
06	33.4	55.7	61.8	57.2	83.1	134.	126.	92.0	61.6	44.5	34.2	46.1
07	32.6	55.7	61.8	57.2	86.9	129.	125.	89.5	61.6	43.6	33.4	46.1
08	32.6	55.7	61.8	57.2	86.9	134.	126.	85.7	60.3	41.7	31.8	44.1
09	33.4	55.7	58.7	57.2	148.	179.	126.	85.7	60.3	40.7	31.0	44.1
10	33.4	53.8	55.7	57.2	175.	164.	122.	84.4	60.3	39.8	31.0	44.1
11	33.4	49.9	57.2	57.2	389.	153.	119.	80.6	60.3	37.9	31.0	44.1
12	32.6	48.0	57.2	57.2	568.	147.	119.	80.6	60.3	37.9	31.0	44.1
13	32.6	48.0	57.2	57.2	408.	165.	119.	80.6	60.3	36.9	31.0	42.2
14	31.8	48.0	57.2	57.2	278.	400.	119.	80.6	60.3	36.9	31.0	40.3
15	30.2	49.9	57.2	57.2	223.	384.	123.	78.1	60.3	36.9	30.2	40.3
16	31.8	49.9	57.2	57.2	184.	299.	133.	78.1	60.3	37.9	30.2	40.3
17	32.6	49.9	57.2	57.2	162.	269.	133.	75.5	57.8	37.9	30.2	40.3
18	32.6	57.2	57.2	57.2	150.	248.	128.	75.5	55.3	37.9	30.2	40.3
19	32.6	61.8	57.2	57.2	142.	239.	119.	73.0	54.0	36.9	30.2	40.3
20	32.6	61.8	57.2	57.2	136.	214.	117.	71.7	53.1	36.9	97.3	40.3
21	32.6	61.8	57.2	57.2	129.	186.	117.	73.0	54.0	36.9	44.1	40.3
22	33.4	61.8	57.2	57.2	123.	170.	112.	71.7	52.1	36.9	44.1	40.3
23	33.4	61.8	57.2	57.2	117.	165.	114.	70.5	52.1	36.0	44.1	48.0
24	32.6	74.0	57.2	57.2	115.	165.	117.	70.5	50.2	35.0	44.1	48.0
25	32.6	79.0	57.2	226.	117.	188.	114.	70.5	50.2	36.0	44.1	53.8
26	31.8	77.0	57.2	295.	115.	175.	108.	70.5	49.3	35.0	44.1	77.0
27	31.0	72.4	57.2	154.	209.	165.	101.	66.7	49.3	34.2	44.1	63.3
28	31.0	70.9	57.2	126.	159.	156.	99.8	66.7	48.3	33.4	44.1	57.2
29	31.0	70.9	57.2	112.	-----	151.	96.7	65.4	47.4	33.4	44.1	49.9
30	31.0	69.4	57.2	101.	-----	147.	93.6	64.1	45.5	33.4	44.1	48.0
31	31.0	-----	57.2	92.0	-----	145.	-----	64.1	-----	34.2	44.1	-----
Maks.	39.8	87.1	69.4	539.	685.	626.	145.	106.	64.1	44.5	162.	109.
Min.	30.2	31.0	55.7	57.2	79.3	125.	90.7	62.9	45.5	33.4	30.2	40.3
Ortalama	32.6	57.1	59.0	80.0	169.	187.	120.	78.6	56.5	38.2	38.4	46.5
LT/SN/Km2	14.0	24.5	25.3	34.3	72.4	80.3	51.7	33.8	24.2	16.4	16.5	20.0
AKIM mm.	37.5	63.6	67.8	91.9	175.	215.	134.	90.4	62.9	43.9	44.1	51.7
MİL. M3	87.4	148.	158.	214.	408.	501.	312.	211.	146.	102.	103.	121.

SU YILI (2006) YILLIK TOPLAM AKIM 2511.40 MİLYON M3 1078 MM. 34.2 LT/SN/Km2

09. Antalya Havzasi

D09A104 BEYBASAN D. AHIRTAŞ

YERİ : ANTALYA-BURDUR KARAYOLUNU 22. KM SONRA SAĞA SAPILIR.SIRASIYLA KARATAŞ-CAMİLI-KILLIKTE 12 KM SONRA KÖPRÜ GEÇILMEDEN SAĞA DÖNÜLÜR VE 1 KM SONRA İSTASYONA VARILIR. 30°44'3" Doğu - 37°12'10" Kuzey

YAĞIŞ ALANI : 12,75 km2 YAKLAŞIK KOT : 403 m

GÖZLEM SÜRESİ : 01.10.1992 - 30.09.2006

ORTALAMA AKIMLAR : Gözlem süresinde 0.116 m3/sn. (14 Yıllık) 2006 Su yılında 0.040 m3/sn.

ANLIK EN ÇOK VE EN AZ AKIMLAR:

2006 Su yılında anlık ençok akım	:	5.10	m3/sn	07.02.2006
2006 Su yılında anlık enaz akım	:	0.000	m3/sn	01.10.2005
Gözlem süresinde anlık ençok akım	:	125.	m3/sn	08.01.1997
Gözlem süresinde anlık enaz akım	:	0.000	m3/sn	01.10.1992

Akımlar 01 Ekim 2005 'den 30 Eylül 2006' a kadar m3/sn olarak

Gün	Ekim	Kasım	Aralık	Ocak	Şubat	Mart	Nisan	Mayıs	Haziran	Temmuz	Ağustos	Eylül
01	KURU	KURU	KURU	0.091	0.064	0.115	0.023	0.005	0.005	KURU	KURU	KURU
02	KURU	KURU	KURU	0.091	0.040	0.115	0.023	0.005	0.005	KURU	KURU	KURU
03	KURU	KURU	KURU	0.064	0.040	0.185	0.023	0.005	0.005	KURU	KURU	KURU
04	KURU	KURU	KURU	0.064	0.040	0.150	0.023	0.005	0.005	KURU	KURU	KURU
05	KURU	KURU	KURU	0.064	0.040	0.115	0.023	0.005	0.005	KURU	KURU	KURU
06	KURU	KURU	KURU	0.064	0.064	0.115	0.023	0.005	0.005	KURU	KURU	KURU
07	KURU	KURU	KURU	0.091	0.370	0.115	0.023	0.005	0.005	KURU	KURU	KURU
08	KURU	KURU	KURU	0.091	0.860	0.115	0.023	0.005	0.005	KURU	KURU	KURU
09	KURU	KURU	KURU	0.091	0.420	0.185	0.023	0.005	0.005	KURU	KURU	KURU
10	KURU	KURU	KURU	0.091	0.220	0.115	0.023	0.005	0.005	KURU	KURU	KURU
11	KURU	KURU	KURU	0.091	0.185	0.115	0.023	0.005	0.005	KURU	KURU	KURU
12	KURU	KURU	KURU	0.091	0.150	0.150	0.023	0.005	0.005	KURU	KURU	KURU
13	KURU	KURU	KURU	0.064	0.150	0.500	0.023	0.005	0.005	KURU	KURU	KURU
14	KURU	KURU	KURU	0.064	0.115	1.15	0.023	0.005	0.005	KURU	KURU	KURU
15	KURU	KURU	KURU	0.064	0.115	0.550	0.023	0.005	0.005	KURU	KURU	KURU
16	KURU	KURU	KURU	0.064	0.115	0.370	0.023	0.005	0.001	KURU	KURU	KURU
17	KURU	KURU	KURU	0.064	0.084	0.260	0.023	0.005	0.001	KURU	KURU	KURU
18	KURU	KURU	KURU	0.064	0.084	0.220	0.005	0.005	0.001	KURU	KURU	KURU
19	KURU	KURU	KURU	0.064	0.084	0.185	0.005	0.005	0.001	KURU	KURU	KURU
20	KURU	KURU	KURU	0.064	0.084	0.150	0.005	0.005	KURU	KURU	KURU	KURU
21	KURU	KURU	KURU	0.064	0.084	0.150	0.005	0.005	KURU	KURU	KURU	KURU
22	KURU	KURU	KURU	0.064	0.084	0.115	0.005	0.005	KURU	KURU	KURU	KURU
23	KURU	KURU	KURU	0.260	0.084	0.115	0.005	0.005	KURU	KURU	KURU	KURU
24	KURU	KURU	KURU	0.500	0.084	0.084	0.005	0.005	KURU	KURU	KURU	KURU
25	KURU	KURU	KURU	0.690	0.084	0.084	0.005	0.005	KURU	KURU	KURU	KURU
26	KURU	KURU	KURU	0.220	0.115	0.084	0.005	0.005	KURU	KURU	KURU	KURU
27	KURU	KURU	KURU	0.115	0.150	0.048	0.005	0.005	KURU	KURU	KURU	KURU
28	KURU	KURU	0.040	0.091	0.115	0.048	0.005	0.005	KURU	KURU	KURU	KURU
29	KURU	KURU	0.115	0.064	-----	0.048	0.005	0.005	KURU	KURU	KURU	KURU
30	KURU	KURU	0.115	0.064	-----	0.048	0.005	0.005	KURU	KURU	KURU	KURU
31	KURU	-----	0.091	0.064	-----	0.048	-----	0.005	-----	KURU	KURU	-----
Maks.	KURU	KURU	0.115	2.70	5.10	2.70	0.048	0.023	0.005	KURU	KURU	KURU
Min.	KURU	KURU	KURU	0.064	0.040	0.048	0.005	0.001	KURU	KURU	KURU	KURU
Ortalama	KURU	KURU	0.012	0.119	0.147	0.189	0.015	0.005	0.003	KURU	KURU	KURU
LT/SN/Km2	0.000	0.000	0.913	9.34	11.6	14.8	1.19	0.392	0.207	0.000	0.000	0.000
AKIM mm.	0.000	0.000	2.45	25.0	27.9	39.6	3.09	1.05	0.535	0.000	0.000	0.000
MİL. M3	0.000	0.000	0.031	0.319	0.356	0.505	0.039	0.013	0.007	0.000	0.000	0.000

SU YILI (2006) YILLIK TOPLAM AKIM 1.27 MİLYON M3 100 MM. 3.2 LT/SN/Km2

09. Antalya Havzasi

D09A111 DOYRAN D. DOYRAN

YERİ : **ANTALYA MERKEZ ÇAKIRLAR YOLUNDAN DOYRAN A 1 KM KALA SAKLIKENT YOL AYRIMINA VARILIR BU GÜZERGAHTAN 2 KM SONRA SOLA DÖNÜLÜR VE YAKLAŞIK 5 KM SONRA İSTASYONA VARILIR. 30°30'43" Doğu - 36°53'23" Kuzey**

YAĞIŞ ALANI : 105,80 km2 **YAKLAŞIK KOT : 145 m**

GÖZLEM SÜRESİ : 01.10.1993 - **30.09.2006**

ORTALAMA AKIMLAR : Gözlem süresinde 0.924 m3/sn. (12 Yıllık) 2006 Su yılında 0.421 m3/sn.

ANLIK EN ÇOK VE EN AZ AKIMLAR:

2006 Su yılında anlık ençok akım	:	**18.7**	**m3/sn**	**15.04.2006**
2006 Su yılında anlık enaz akım	:	**0.004**	**m3/sn**	**08.09.2006**
Gözlem süresinde anlık ençok akım	:	**62.0**	**m3/sn**	**25.12.2003**
Gözlem süresinde anlık enaz akım	:	**0.000**	**m3/sn**	**31.10.1995**

Akımlar 01 Ekim 2005 'den 30 Eylül 2006' a kadar m3/sn olarak

Gün	Ekim	Kasım	Aralık	Ocak	Şubat	Mart	Nisan	Mayıs	Haziran	Temmuz	Ağustos	Eylül
01	0.038	0.038	0.038	0.194	0.194	0.194	1.53	2.88	0.069	0.008	0.038	0.038
02	0.038	0.038	0.038	0.130	0.194	0.258	1.53	2.35	0.069	0.008	0.038	0.038
03	0.038	0.038	0.038	0.130	0.194	0.258	1.41	2.00	0.069	0.008	0.069	0.026
04	0.038	0.099	0.038	0.130	0.130	0.386	1.29	1.65	0.069	0.008	0.069	0.026
05	0.038	0.069	0.038	0.130	0.130	0.258	1.41	1.65	0.099	0.008	0.069	0.026
06	0.038	0.099	0.038	0.130	0.194	0.130	1.29	1.65	0.069	0.008	0.069	0.026
07	0.026	0.099	0.038	0.130	0.194	0.099	1.41	1.53	0.069	0.014	0.069	0.026
08	0.026	0.099	0.069	0.130	0.570	0.130	1.41	1.53	0.069	0.038	0.069	0.008
09	0.026	0.099	0.069	0.130	0.386	0.099	1.29	1.17	0.069	0.038	0.069	0.004
10	0.026	0.038	0.069	0.130	0.386	0.069	1.29	1.17	0.069	0.038	0.069	0.004
11	0.026	0.038	0.069	0.130	0.322	0.069	1.29	0.930	0.069	0.038	0.069	0.004
12	0.069	0.038	0.069	0.130	0.322	0.069	1.17	0.810	0.038	0.038	0.038	0.004
13	0.099	0.038	0.069	0.130	0.322	2.53	1.29	0.690	0.038	0.038	0.038	0.004
14	0.099	0.038	0.069	0.130	0.322	2.70	1.29	0.690	0.026	0.038	0.038	0.004
15	0.099	0.038	0.069	0.130	0.322	1.83	3.23	0.450	0.026	0.038	0.038	0.004
16	0.130	0.038	0.069	0.130	0.194	1.41	5.72	0.450	0.026	0.038	0.026	0.004
17	0.130	0.038	0.069	0.130	0.099	1.29	4.03	0.450	0.026	0.038	0.014	0.004
18	0.099	0.069	0.069	0.130	0.099	1.17	4.03	0.450	0.026	0.038	0.014	0.004
19	0.099	0.038	0.069	0.130	0.099	1.17	3.82	0.450	0.026	0.038	0.014	0.004
20	0.130	0.194	0.069	0.130	0.099	1.17	3.61	0.386	0.026	0.038	0.014	0.004
21	0.130	0.069	0.069	0.130	0.099	1.17	3.40	0.258	0.026	0.038	0.014	0.008
22	0.130	0.038	0.038	0.130	0.099	1.29	3.23	0.130	0.026	0.038	0.014	0.008
23	0.130	0.038	0.099	0.450	0.130	1.65	3.05	0.130	0.026	0.038	0.014	0.008
24	0.099	0.038	0.194	0.450	0.130	1.65	3.05	0.130	0.026	0.038	0.014	0.008
25	0.069	0.038	0.258	0.450	0.130	1.53	3.05	0.130	0.026	0.038	0.014	0.008
26	0.026	0.038	0.258	0.322	0.194	1.53	3.05	0.099	0.014	0.038	0.014	0.008
27	0.026	0.038	0.258	0.258	0.194	1.65	3.05	0.130	0.014	0.038	0.014	0.008
28	0.026	0.038	0.322	0.258	0.194	2.00	2.88	0.099	0.014	0.038	0.026	0.008
29	0.026	0.038	0.258	0.194	-----	1.65	2.88	0.099	0.014	0.038	0.026	0.008
30	0.038	0.038	0.258	0.194	-----	1.65	2.88	0.069	0.014	0.038	0.038	0.008
31	0.038	-----	0.258	0.194	-----	1.65	-----	0.069	-----	0.038	0.038	-----
Maks.	0.130	0.810	0.322	0.570	2.70	7.01	18.7	2.88	0.099	0.038	0.069	0.570
Min.	0.026	0.038	0.038	0.130	0.099	0.069	1.05	0.069	0.014	0.008	0.014	0.004
Ortalama	0.066	0.056	0.111	0.184	0.212	1.06	2.46	0.796	0.042	0.031	0.037	0.011
LT/SN/Km2	0.625	0.534	1.05	1.74	2.01	9.97	23.3	7.52	0.393	0.297	0.353	0.108
AKIM mm.	1.67	1.38	2.80	4.65	4.85	26.7	60.3	20.2	1.02	0.795	0.945	0.279
MİL. M3	0.177	0.146	0.297	0.492	0.513	2.83	6.38	2.13	0.108	0.084	0.100	0.030

SU YILI (2006) YILLIK TOPLAM AKIM 13.29 MİLYON M3 126 MM. 4.0 LT/SN/Km2

09. Antalya Havzasi

D09A114 KİZILLAR D. YAVRUDOGAN

YERİ : **ANTALYA-MANAVGAT YOLU PERİ KÖYÜNDEN 300 M SONRA YAVRUDOĞAN KÖY YOLUNA DÖNÜLÜR 10 KM SONRA KÖY İÇINDEDIR.**
31°18'45" Doğu - 36°53'14" Kuzey

YAĞIŞ ALANI : 22,54 km2 **YAKLAŞIK KOT :** 75 m

GÖZLEM SÜRESİ : 01.10.1998 - **30.09.2006**

ORTALAMA AKIMLAR : Gözlem süresinde 0.228 m3/sn. (8 Yıllık) 2006 Su yılında 0.100 m3/sn.

ANLIK EN ÇOK VE EN AZ AKIMLAR:

2006 Su yılında anlık ençok akım	:	18.1	m3/sn	20.11.2005
2006 Su yılında anlık enaz akım	:	0.000	m3/sn	01.10.2005
Gözlem süresinde anlık ençok akım	:	55.8	m3/sn	07.02.2003
Gözlem süresinde anlık enaz akım	:	0.000	m3/sn	01.10.1998

Akımlar 01 Ekim 2005 'den 30 Eylül 2006' a kadar m3/sn olarak

Gün	Ekim	Kasım	Aralık	Ocak	Şubat	Mart	Nisan	Mayıs	Haziran	Temmuz	Ağustos	Eylül
01	KURU	0.004	0.021	0.024	0.123	0.295	0.145	0.123	0.005	0.002	KURU	KURU
02	KURU	0.004	0.021	0.021	0.123	0.295	0.145	0.100	0.005	0.002	KURU	KURU
03	KURU	0.006	0.024	0.018	0.100	0.295	0.145	0.085	0.007	0.002	KURU	KURU
04	KURU	0.038	0.024	0.021	0.100	0.260	0.123	0.070	0.005	0.001	KURU	KURU
05	KURU	0.011	0.024	0.021	0.085	0.260	0.145	0.085	0.002	KURU	KURU	KURU
06	KURU	0.011	0.024	0.085	0.168	0.260	0.145	0.085	0.004	KURU	KURU	KURU
07	KURU	0.008	0.024	0.059	0.550	0.260	0.145	0.100	0.005	KURU	KURU	KURU
08	KURU	0.007	0.024	0.049	1.30	0.260	0.145	0.085	0.006	KURU	KURU	KURU
09	KURU	0.007	0.024	0.027	0.665	0.260	0.123	0.070	0.005	KURU	KURU	KURU
10	KURU	0.007	0.024	0.027	0.450	0.225	0.123	0.049	0.002	KURU	KURU	KURU
11	KURU	0.006	0.024	0.038	0.550	0.225	0.145	0.049	0.004	KURU	KURU	KURU
12	0.002	0.005	0.027	0.027	1.01	0.225	0.145	0.038	0.003	KURU	KURU	KURU
13	0.007	0.005	0.027	0.027	0.400	0.190	0.145	0.024	0.002	KURU	KURU	KURU
14	0.006	0.005	0.038	0.027	0.295	0.190	0.145	0.027	0.003	KURU	KURU	KURU
15	0.006	0.005	0.085	0.024	0.295	0.190	0.190	0.027	KURU	KURU	KURU	KURU
16	0.049	0.005	0.070	0.024	0.295	0.190	0.330	0.024	KURU	KURU	KURU	KURU
17	0.014	0.004	0.059	0.024	0.295	0.190	0.145	0.024	0.001	KURU	KURU	KURU
18	0.008	0.018	0.123	0.024	0.295	0.145	0.123	0.024	0.003	KURU	KURU	KURU
19	0.007	0.190	0.225	0.024	0.295	0.145	0.123	0.021	0.003	KURU	KURU	KURU
20	0.007	3.89	0.059	0.027	0.295	0.145	0.100	0.018	0.003	KURU	KURU	KURU
21	0.007	0.225	0.049	0.024	0.295	0.145	0.123	0.014	0.004	KURU	KURU	KURU
22	0.007	0.085	0.049	0.027	0.295	0.145	0.123	0.011	0.003	KURU	KURU	KURU
23	0.006	0.059	0.038	0.049	0.295	0.145	0.123	0.018	0.004	KURU	KURU	KURU
24	0.006	0.049	0.038	3.04	0.295	0.145	0.145	0.011	0.004	KURU	KURU	KURU
25	0.005	0.038	0.038	2.93	0.295	0.145	0.123	0.007	0.002	KURU	KURU	KURU
26	0.005	0.027	0.027	0.730	0.295	0.145	0.123	0.007	0.003	KURU	KURU	KURU
27	0.005	0.024	0.027	0.365	0.295	0.145	0.145	0.007	0.004	KURU	KURU	KURU
28	0.005	0.024	0.027	0.260	0.295	0.145	0.145	0.008	0.002	KURU	KURU	KURU
29	0.005	0.021	0.024	0.190	-----	0.145	0.145	0.007	0.001	KURU	KURU	KURU
30	0.005	0.021	0.021	0.168	-----	0.145	0.123	0.004	0.002	KURU	KURU	KURU
31	0.004	-----	0.024	0.145	-----	0.145	-----	0.006	-----	KURU	KURU	-----
Maks.	1.70	18.1	1.01	11.0	7.93	0.450	0.795	0.225	0.011	0.002	KURU	KURU
Min.	KURU	0.003	0.021	0.018	0.085	0.145	0.100	0.003	KURU	KURU	KURU	KURU
Ortalama	0.005	0.160	0.043	0.276	0.359	0.197	0.143	0.040	0.003	0.000	KURU	KURU
LT/SN/Km2	0.238	7.11	1.91	12.2	15.9	8.73	6.35	1.76	0.143	0.010	0.000	0.000
AKIM mm.	0.636	18.4	5.11	32.8	38.5	23.4	16.5	4.71	0.372	0.027	0.000	0.000
MİL. M3	0.014	0.415	0.115	0.738	0.868	0.527	0.371	0.106	0.008	0.001	0.000	0.000

SU YILI (2006) YILLIK TOPLAM AKIM 3.16 MİLYON M3 140 MM. 4.5 LT/SN/Km2

09. Antalya Havzasi

D09A116 NARAS D. ŞİŞELER

YERİ : ANTALYA MANAVGAT ŞELALESİ İSTİKAMETİNDE DOLBOZLAR KÖYÜNE ORADANDA ŞİŞELERE VARILIR
2 KM SONRA İSTASYONA VARILIR.
31°24'15" Doğu - 36°52'25" Kuzey

YAĞIŞ ALANI : 193,90 km2 YAKLAŞIK KOT : 30 m

GÖZLEM SÜRESİ : 01.10.1999 - 30.09.2006

ORTALAMA AKIMLAR : Gözlem süresinde 3.494 m3/sn. (7 Yıllık) 2006 Su yılında 1.793 m3/sn.

ANLIK EN ÇOK VE EN AZ AKIMLAR:

2006 Su yılında anlık ençok akım	:	118.	m3/sn	20.11.2005
2006 Su yılında anlık enaz akım	:	0.000	m3/sn	01.10.2005
Gözlem süresinde anlık ençok akım	:	425.	m3/sn	17.12.2001
Gözlem süresinde anlık enaz akım	:	0.000	m3/sn	01.10.1999

99. Anahtar Eğrisi (Seviyeler cm olarak)

Seviye	Akım	Seviye	Akım	Seviye	Akım	Seviye	Akım
10	0.000	81	0.543	200	98.5	370	433.
50	0.000	85	0.966	240	165.	380	455.
68	0.015	89	1.6	280	243.	390	477.
73	0.113	120	13.1	320	327.	400	499.
77	0.272	160	47.2	360	411.	410	522.

Akımlar 01 Ekim 2005 'den 30 Eylül 2006' a kadar m3/sn olarak

Gün	Ekim	Kasım	Aralık	Ocak	Şubat	Mart	Nisan	Mayıs	Haziran	Temmuz	Ağustos	Eylül
01	KURU	0.137	0.817	1.40	4.72	2.88	3.25	1.40	0.700	0.090	KURU	KURU
02	KURU	0.137	0.817	1.40	4.00	2.88	3.25	1.40	0.393	0.057	KURU	KURU
03	KURU	0.205	0.570	1.40	3.63	2.88	3.25	1.40	0.393	0.048	KURU	KURU
04	KURU	0.933	0.570	1.28	3.44	2.69	3.25	1.40	0.393	0.048	KURU	KURU
05	KURU	0.393	0.570	1.28	3.25	2.50	3.25	1.40	0.393	0.048	KURU	KURU
06	KURU	0.298	0.570	1.28	3.63	2.50	3.25	1.28	0.393	0.113	KURU	KURU
07	KURU	0.298	0.570	1.28	4.72	2.23	3.25	1.28	0.393	0.298	KURU	KURU
08	KURU	0.250	0.570	1.28	4.72	2.50	3.25	1.28	0.393	0.160	KURU	KURU
09	KURU	0.160	0.817	1.28	24.0	4.72	3.06	1.28	0.298	0.113	KURU	KURU
10	KURU	0.160	0.700	1.28	14.6	4.96	3.06	1.28	0.298	0.057	KURU	KURU
11	0.066	0.160	0.700	1.28	13.1	4.00	3.06	1.28	0.298	0.048	KURU	KURU
12	0.298	0.113	0.817	1.28	13.1	3.63	2.88	1.17	0.250	0.048	KURU	KURU
13	0.250	0.113	0.817	1.28	13.1	3.44	2.88	1.17	0.160	0.039	KURU	KURU
14	0.205	0.113	1.05	1.17	12.6	3.44	2.69	1.17	0.160	0.030	KURU	KURU
15	0.205	0.113	2.23	1.17	12.6	3.63	2.69	1.17	0.160	0.015	KURU	KURU
16	0.933	0.113	1.95	1.17	10.2	3.63	5.20	1.17	0.137	0.015	KURU	KURU
17	0.345	0.113	1.68	1.05	8.80	3.63	4.00	1.17	0.137	0.007	KURU	KURU
18	0.298	0.393	5.92	1.05	6.88	3.63	3.25	1.17	0.113	KURU	KURU	KURU
19	0.250	2.50	16.0	1.05	6.16	3.81	3.06	1.17	0.113	KURU	KURU	KURU
20	0.250	24.0	12.2	1.17	5.44	3.81	3.06	1.17	0.090	KURU	KURU	KURU
21	0.250	3.81	5.20	1.17	4.96	3.81	2.69	1.17	0.090	KURU	KURU	KURU
22	0.250	2.69	4.00	1.17	4.48	4.48	2.69	1.17	0.090	KURU	KURU	KURU
23	0.205	2.23	3.63	1.17	4.00	4.72	2.69	1.17	0.066	KURU	KURU	KURU
24	0.205	1.95	3.44	1.17	3.81	4.24	2.50	1.17	0.066	KURU	KURU	KURU
25	0.160	1.68	2.88	1.28	3.44	4.24	2.23	1.05	0.057	KURU	KURU	KURU
26	0.160	1.28	2.69	1.28	3.44	4.00	1.95	1.05	0.057	KURU	KURU	4.72
27	0.160	1.05	2.50	3.81	3.44	3.81	1.95	1.05	0.048	KURU	KURU	1.68
28	0.160	1.05	2.23	10.7	3.06	4.00	1.95	0.933	0.048	KURU	KURU	1.05
29	0.160	0.817	1.95	7.84	-----	3.63	1.95	0.933	0.048	KURU	KURU	0.440
30	0.160	0.817	1.68	5.92	-----	3.25	1.68	0.933	0.160	KURU	KURU	0.440
31	0.137	-----	1.68	4.96	-----	3.25	-----	0.933	-----	KURU	KURU	-----
Maks.	8.80	118.	28.5	14.1	32.1	7.36	8.32	1.68	0.933	0.298	KURU	4.72
Min.	KURU	0.113	0.570	1.05	2.88	2.23	1.68	0.933	0.048	KURU	KURU	KURU
Ortalama	0.165	1.60	2.64	2.11	7.26	3.57	2.91	1.19	0.213	0.040	KURU	0.278
LT/SN/Km2	0.850	8.26	13.6	10.9	37.4	18.4	15.0	6.12	1.10	0.205	0.000	1.43
AKIM mm.	2.28	21.4	36.5	29.1	90.6	49.4	38.8	16.4	2.85	0.550	0.000	3.71
MİL. M3	0.441	4.15	7.07	5.64	17.6	9.57	7.53	3.18	0.553	0.107	0.000	0.720

SU YILI (2006) YILLIK TOPLAM AKIM 56.56 MİLYON M3 292 MM. 9.2 LT/SN/Km2

09. Antalya Havzasi

D09A117 ALİCI D. GÜNDOGMUS

YERİ : **ANTALYA - ALANYA İSTIKAMETINDE GIDILEREK ALARAHAN YOLUNA SAPILIR.ORADAN 17 KM SONRA İSTASYONA VARILIR.**
31°47'21" Doğu - 36°42'33" Kuzey

YAĞIŞ ALANI : 10,03 km2 **YAKLAŞIK KOT :** 392 m

GÖZLEM SÜRESİ : 01.10.2000 - 30.09.2006

ORTALAMA AKIMLAR : Gözlem süresinde 0.011 m3/sn. (6 Yıllık) 2006 Su yılında 0.003 m3/sn.

ANLIK EN ÇOK VE EN AZ AKIMLAR:

2006 Su yılında anlık ençok akım	:	0.281 m3/sn	06.02.2006
2006 Su yılında anlık enaz akım	:	0.000 m3/sn	01.10.2005
Gözlem süresinde anlık ençok akım	:	5.40 m3/sn	27.12.2001
Gözlem süresinde anlık enaz akım	:	0.000 m3/sn	01.10.2000

Akımlar 01 Ekim 2005 'den 30 Eylül 2006' a kadar m3/sn olarak

Gün	Ekim	Kasım	Aralık	Ocak	Şubat	Mart	Nisan	Mayıs	Haziran	Temmuz	Ağustos	Eylül
01	KURU	KURU	KURU	KURU	0.002	0.004	0.007	0.004	KURU	KURU	KURU	KURU
02	KURU	KURU	KURU	KURU	0.002	0.004	0.007	0.007	KURU	KURU	KURU	KURU
03	KURU	KURU	KURU	KURU	0.002	0.004	0.007	0.007	KURU	KURU	KURU	KURU
04	KURU	KURU	KURU	KURU	0.002	0.004	0.007	0.004	KURU	KURU	KURU	KURU
05	KURU	KURU	KURU	KURU	0.011	0.004	0.007	0.004	KURU	KURU	KURU	KURU
06	KURU	KURU	KURU	KURU	0.083	0.004	0.007	0.004	KURU	KURU	KURU	KURU
07	KURU	KURU	KURU	KURU	0.046	0.004	0.007	0.004	KURU	KURU	KURU	KURU
08	KURU	KURU	KURU	KURU	0.029	0.004	0.007	0.002	KURU	KURU	KURU	KURU
09	KURU	KURU	KURU	KURU	0.016	0.011	0.007	0.004	KURU	KURU	KURU	KURU
10	KURU	KURU	KURU	KURU	0.011	0.011	0.007	0.004	KURU	KURU	KURU	KURU
11	KURU	KURU	KURU	KURU	0.011	0.007	0.007	0.004	KURU	KURU	KURU	KURU
12	KURU	KURU	KURU	KURU	0.011	0.007	0.007	0.004	KURU	KURU	KURU	KURU
13	KURU	KURU	KURU	KURU	0.007	0.007	0.007	0.004	KURU	KURU	KURU	KURU
14	KURU	KURU	KURU	KURU	0.007	0.016	0.007	0.002	KURU	KURU	KURU	KURU
15	KURU	KURU	KURU	KURU	0.007	0.011	0.007	0.002	KURU	KURU	KURU	KURU
16	KURU	KURU	KURU	KURU	0.007	0.011	0.007	0.002	KURU	KURU	KURU	KURU
17	KURU	KURU	KURU	KURU	0.007	0.011	0.007	0.002	KURU	KURU	KURU	KURU
18	KURU	KURU	KURU	KURU	0.007	0.011	0.007	0.001	KURU	KURU	KURU	KURU
19	KURU	KURU	KURU	0.002	0.007	0.011	0.007	0.001	KURU	KURU	KURU	KURU
20	KURU	KURU	KURU	0.004	0.007	0.011	0.007	0.004	KURU	KURU	KURU	KURU
21	KURU	KURU	KURU	0.002	0.007	0.011	0.007	0.002	KURU	KURU	KURU	KURU
22	KURU	KURU	KURU	0.002	0.007	0.011	0.007	0.001	KURU	KURU	KURU	KURU
23	KURU	KURU	KURU	0.007	0.004	0.011	0.007	0.001	KURU	KURU	KURU	KURU
24	KURU	KURU	KURU	0.011	0.004	0.011	0.004	KURU	KURU	KURU	KURU	KURU
25	KURU	KURU	KURU	0.016	0.004	0.011	0.004	KURU	KURU	KURU	KURU	KURU
26	KURU	KURU	KURU	0.004	0.004	0.011	0.007	KURU	KURU	KURU	KURU	KURU
27	KURU	KURU	KURU	0.002	0.004	0.011	0.004	KURU	KURU	KURU	KURU	KURU
28	KURU	KURU	KURU	0.002	0.004	0.011	0.007	KURU	KURU	KURU	KURU	KURU
29	KURU	KURU	KURU	0.002	-----	0.011	0.004	KURU	KURU	KURU	KURU	KURU
30	KURU	KURU	KURU	0.002	-----	0.007	0.007	KURU	KURU	KURU	KURU	KURU
31	KURU	-----	KURU	0.002	-----	0.007	-----	KURU	-----	KURU	KURU	-----
Maks.	KURU	KURU	KURU	0.029	0.281	0.057	0.011	0.007	KURU	KURU	KURU	KURU
Min.	KURU	KURU	KURU	KURU	0.002	0.004	0.002	KURU	KURU	KURU	KURU	KURU
Ortalama	KURU	KURU	KURU	0.002	0.011	0.009	0.007	0.002	KURU	KURU	KURU	KURU
LT/SN/Km2	0.000	0.000	0.000	0.187	1.14	0.868	0.658	0.238	0.000	0.000	0.000	0.000
AKIM mm.	0.000	0.000	0.000	0.500	2.76	2.33	1.71	0.637	0.000	0.000	0.000	0.000
MİL. M3	0.000	0.000	0.000	0.005	0.028	0.023	0.017	0.006	0.000	0.000	0.000	0.000

SU YILI (2006) YILLIK TOPLAM AKIM 0.08 MİLYON M3 8 MM. 0.3 LT/SN/Km2

09. Antalya Havzasi

D09A118 Bogalak D. Tasagil

YERİ : **ANTALYA MANAVGAT İSTIKAMETINDEN GIDILEREK TAŞAĞIL YOL AYRIMINDAN SAPILARAK TAŞAĞILA VARILIR.TAŞAĞILDAN 4 KM SONRA İSTASYONA VARILIR.**
31°15'48" Doğu - 36°55'52" Kuzey

YAĞIŞ ALANI : 5,30 km2 **YAKLAŞIK KOT :** 75 m

GÖZLEM SÜRESİ : 01.10.2000 - **30.09.2006**

ORTALAMA AKIMLAR : Gözlem süresinde 0.102 m3/sn. (6 Yıllık) 2006 Su yılında 0.096 m3/sn.

ANLIK EN ÇOK VE EN AZ AKIMLAR:

2006 Su yılında anlık ençok akım	:	**21.8**	m3/sn	**20.11.2005**
2006 Su yılında anlık enaz akım	:	**0.000**	m3/sn	**01.10.2005**
Gözlem süresinde anlık ençok akım	:	**21.8**	m3/sn	**20.11.2005**
Gözlem süresinde anlık enaz akım	:	**0.000**	m3/sn	**01.10.2000**

Akımlar 01 Ekim 2005 'den 30 Eylül 2006' a kadar m3/sn olarak

Gün	Ekim	Kasım	Aralık	Ocak	Şubat	Mart	Nisan	Mayıs	Haziran	Temmuz	Ağustos	Eylül
01	KURU	KURU	0.096	0.018	0.222	0.188	0.049	0.018	0.002	KURU	KURU	KURU
02	KURU	KURU	0.096	0.018	0.222	0.188	0.049	0.010	0.001	KURU	KURU	KURU
03	KURU	KURU	0.049	0.018	0.188	0.188	0.049	0.010	0.001	KURU	KURU	KURU
04	KURU	KURU	0.049	0.018	0.188	0.120	0.049	0.010	0.001	KURU	KURU	KURU
05	KURU	KURU	0.049	0.018	0.188	0.120	0.049	0.010	0.001	KURU	KURU	KURU
06	KURU	KURU	0.018	0.018	0.324	0.025	0.049	0.010	0.001	KURU	KURU	KURU
07	KURU	KURU	0.018	0.018	0.652	0.018	0.025	0.010	KURU	KURU	KURU	KURU
08	KURU	KURU	0.018	0.018	0.892	0.018	0.025	0.008	KURU	KURU	KURU	KURU
09	KURU	KURU	0.018	0.018	0.556	0.049	0.025	0.008	KURU	KURU	KURU	KURU
10	KURU	KURU	0.018	0.018	0.426	0.018	0.025	0.008	KURU	KURU	KURU	KURU
11	KURU	KURU	0.018	0.018	0.460	0.018	0.025	0.008	KURU	KURU	KURU	KURU
12	KURU	KURU	0.018	0.018	0.892	0.025	0.025	0.008	KURU	KURU	KURU	KURU
13	KURU	KURU	0.018	0.018	0.604	0.025	0.025	0.006	KURU	KURU	KURU	KURU
14	KURU	KURU	0.018	0.018	0.460	0.358	0.025	0.006	KURU	KURU	KURU	KURU
15	KURU	KURU	0.025	0.018	0.426	0.222	0.073	0.006	KURU	KURU	KURU	KURU
16	KURU	KURU	0.018	0.018	0.324	0.188	0.222	0.006	KURU	KURU	KURU	KURU
17	KURU	0.002	0.049	0.018	0.324	0.154	0.049	0.006	KURU	KURU	KURU	KURU
18	KURU	0.556	1.43	0.018	0.324	0.154	0.049	0.006	KURU	KURU	KURU	KURU
19	KURU	4.14	2.36	0.025	0.290	0.120	0.049	0.006	KURU	KURU	KURU	KURU
20	KURU	0.358	0.940	0.018	0.290	0.120	0.025	0.006	KURU	KURU	KURU	KURU
21	KURU	0.222	0.290	0.018	0.256	0.096	0.025	0.006	KURU	KURU	KURU	KURU
22	KURU	0.154	0.154	0.018	0.256	0.096	0.025	0.006	KURU	KURU	KURU	KURU
23	KURU	0.154	0.154	0.096	0.222	0.096	0.025	0.006	KURU	KURU	KURU	KURU
24	KURU	0.120	0.120	3.17	0.222	0.073	0.025	0.006	KURU	KURU	KURU	KURU
25	KURU	0.096	0.120	1.94	0.188	0.049	0.018	0.006	KURU	KURU	KURU	KURU
26	KURU	0.096	0.120	0.604	0.188	0.049	0.018	0.004	KURU	KURU	KURU	KURU
27	KURU	0.096	0.096	0.392	0.188	0.049	0.018	0.004	KURU	KURU	KURU	KURU
28	KURU	0.096	0.073	0.324	0.188	0.049	0.018	0.004	KURU	KURU	KURU	KURU
29	KURU	0.096	0.073	0.290	-----	0.049	0.018	0.004	KURU	KURU	KURU	KURU
30	KURU	0.096	0.049	0.256	-----	0.049	0.018	0.004	KURU	KURU	KURU	KURU
31	KURU	-----	0.049	0.222	-----	0.049	-----	0.004	-----	KURU	KURU	-----
Maks.	5.49	21.8	4.80	8.58	4.61	1.12	0.940	0.018	0.002	KURU	KURU	KURU
Min.	KURU	KURU	0.018	0.018	0.188	0.018	0.018	0.004	KURU	KURU	KURU	KURU
Ortalama	KURU	0.209	0.214	0.248	0.356	0.097	0.039	0.007	0.000	KURU	KURU	KURU
LT/SN/Km2	0.000	39.5	40.3	46.8	67.1	18.4	7.35	1.34	0.044	0.000	0.000	0.000
AKIM mm.	0.000	102.	108.	125.	162.	49.2	19.1	3.59	0.114	0.000	0.000	0.000
MİL. M3	0.000	0.543	0.572	0.665	0.861	0.261	0.101	0.019	0.001	0.000	0.000	0.000

SU YILI (2006) YILLIK TOPLAM AKIM 3.02 MİLYON M3 570 MM. 18.1 LT/SN/Km2

09. Antalya Havzasi

D09A120 GİREN D. ORMANA

YERİ : **MANAVGAT-AKSEKİ YOLUNDAN IBRADIYA SAPAN YOLDAN 22 KM SONRA IBRADIYAYA VARILIR.IBRADI ILE ORMANA (ARDIÇ PINARI) ARASI 3 KM DIR. (ORMANA BAŞ KÖYÜ 15 KM DIR.) ORMANA AGİ ARASI 25 KM DIR.**
31°28'18" Doğu - 37°34'24" Kuzey

YAĞIŞ ALANI : **6,53 km2** **YAKLAŞIK KOT : 995 m**

GÖZLEM SÜRESİ : **01.10.2000 - 30.09.2006**

ORTALAMA AKIMLAR : **Gözlem süresinde 0.146 m3/sn. (6 Yıllık) 2006 Su yılında 0.149 m3/sn.**

ANLIK EN ÇOK VE EN AZ AKIMLAR:

2006 Su yılında anlık ençok akım	**:**	**2.42**	**m3/sn**	**18.12.2005**
2006 Su yılında anlık enaz akım	**:**	**0.001**	**m3/sn**	**01.10.2005**
Gözlem süresinde anlık ençok akım	**:**	**4.24**	**m3/sn**	**01.10.2000**
Gözlem süresinde anlık enaz akım	**:**	**0.000**	**m3/sn**	**01.10.2000**

Akımlar 01 Ekim 2005 'den 30 Eylül 2006' a kadar m3/sn olarak

Gün	Ekim	Kasım	Aralık	Ocak	Şubat	Mart	Nisan	Mayıs	Haziran	Temmuz	Ağustos	Eylül
01	0.001	0.311	0.040	0.076	0.158	0.516	0.158	0.058	0.005	0.001	0.001	0.005
02	0.002	0.311	0.040	0.076	0.130	0.434	0.158	0.058	0.005	0.001	0.001	0.005
03	0.003	0.352	0.040	0.058	0.130	0.434	0.130	0.058	0.005	0.001	0.001	0.005
04	0.003	0.352	0.027	0.058	0.130	0.352	0.112	0.058	0.005	0.001	0.001	0.005
05	0.076	0.475	0.027	0.058	0.158	0.311	0.112	0.040	0.005	0.005	0.001	0.005
06	0.076	0.475	0.027	0.130	0.774	0.270	0.094	0.040	0.005	0.005	0.001	0.005
07	0.094	0.598	0.019	0.158	0.868	0.270	0.094	0.040	0.005	0.001	0.001	0.005
08	0.094	0.598	0.019	0.130	0.727	0.557	0.094	0.040	0.005	0.001	0.001	0.001
09	0.112	0.680	0.019	0.112	0.475	0.598	0.094	0.040	0.005	0.001	0.001	0.001
10	0.112	0.915	0.019	0.112	0.598	0.393	0.094	0.040	0.005	0.001	0.001	0.001
11	0.112	0.821	0.019	0.094	1.28	0.311	0.076	0.040	0.005	0.001	0.001	0.001
12	0.130	0.774	0.019	0.094	1.15	0.393	0.076	0.040	0.005	0.001	0.001	0.001
13	0.130	0.774	0.019	0.094	0.680	0.516	0.076	0.040	0.005	0.001	0.001	0.001
14	0.130	0.727	0.019	0.076	0.475	0.915	0.076	0.027	0.005	0.001	0.001	0.001
15	0.130	0.727	0.058	0.076	0.352	0.680	0.130	0.027	0.005	0.001	0.001	0.001
16	0.130	0.557	0.112	0.058	0.242	0.557	0.393	0.027	0.005	0.001	0.001	0.001
17	0.130	0.434	0.094	0.058	0.242	0.557	0.158	0.027	0.005	0.001	0.001	0.001
18	0.130	0.352	0.962	0.058	0.270	0.598	0.130	0.027	0.005	0.001	0.001	0.001
19	0.130	0.270	0.727	0.130	0.311	0.598	0.112	0.027	0.005	0.001	0.001	0.001
20	0.130	0.270	0.434	0.214	0.311	0.475	0.112	0.011	0.005	0.001	0.001	0.001
21	0.130	0.214	0.242	0.130	0.311	0.393	0.094	0.011	0.005	0.001	0.001	0.001
22	0.130	0.214	0.214	0.112	0.311	0.352	0.094	0.011	0.005	0.001	0.001	0.040
23	0.130	0.130	0.158	0.242	0.352	0.311	0.094	0.011	0.005	0.001	0.001	0.027
24	0.130	0.130	0.130	0.393	0.352	0.270	0.094	0.011	0.005	0.001	0.001	0.027
25	0.158	0.094	0.112	0.774	0.393	0.242	0.076	0.011	0.001	0.001	0.001	0.130
26	0.158	0.058	0.112	0.393	0.434	0.214	0.076	0.011	0.001	0.001	0.001	0.027
27	0.158	0.058	0.112	0.242	0.557	0.214	0.076	0.011	0.019	0.001	0.001	0.019
28	0.214	0.058	0.094	0.214	0.434	0.214	0.076	0.011	0.011	0.001	0.001	0.019
29	0.242	0.040	0.094	0.186	-----	0.186	0.076	0.011	0.005	0.001	0.001	0.019
30	0.242	0.040	0.094	0.158	-----	0.158	0.058	0.005	0.005	0.001	0.001	0.019
31	0.270	-----	0.076	0.158	-----	0.158	-----	0.005	-----	0.001	0.001	-----
Maks.	0.311	1.06	2.42	1.61	2.11	1.41	0.962	0.112	0.774	0.019	0.001	2.19
Min.	0.001	0.040	0.019	0.058	0.130	0.158	0.058	0.001	0.001	0.001	0.001	0.001
Ortalama	0.123	0.394	0.135	0.159	0.450	0.402	0.110	0.028	0.005	0.001	0.001	0.013
LT/SN/Km2	18.9	60.3	20.6	24.3	68.9	61.5	16.8	4.32	0.827	0.193	0.153	1.92
AKIM mm.	50.5	156.	55.3	65.1	167.	165.	43.6	11.6	2.14	0.516	0.410	4.97
MİL. M3	0.330	1.02	0.361	0.425	1.09	1.08	0.285	0.076	0.014	0.003	0.003	0.032

SU YILI (2006) YILLIK TOPLAM AKIM 4.72 MİLYON M3 723 MM. 22.9 LT/SN/Km2

09. Antalya Havzasi

D09A121 BOYALI Ç. DOYRAN

YERİ : ANTALYA-BAHTILI KARAYOLU TAKİP EDILEREK SAKLIKENT YOLUNA SAPILIR. ORADAN DOYRANA VARILIR. YAKLAŞIK 20 KM SONRA SARIAĞAÇ MAH. MEZARLIĞINDAN SAĞA DÖNÜLEREK 1 KM SONRA İST. VARILIR.
30°21'20" Doğu - 36°53'21" Kuzey

YAĞIŞ ALANI : 20,85 km2 YAKLAŞIK KOT : 1327 m

GÖZLEM SÜRESİ : 01.10.2001 - 30.09.2006

ORTALAMA AKIMLAR : Gözlem süresinde 0.265 m3/sn. (5 Yıllık) 2006 Su yılında 0.130 m3/sn.

ANLIK EN ÇOK VE EN AZ AKIMLAR:

2006 Su yılında anlık ençok akım	:	13.9	m3/sn	15.04.2006
2006 Su yılında anlık enaz akım	:	0.003	m3/sn	28.05.2006
Gözlem süresinde anlık ençok akım	:	21.4	m3/sn	11.07.2002
Gözlem süresinde anlık enaz akım	:	0.001	m3/sn	22.02.2005

Akımlar 01 Ekim 2005 'den 30 Eylül 2006' a kadar m3/sn olarak

Gün	Ekim	Kasım	Aralık	Ocak	Şubat	Mart	Nisan	Mayıs	Haziran	Temmuz	Ağustos	Eylül
01	0.007	0.024	0.050	0.007	0.140	0.090	0.600	0.480	0.007	0.007	0.007	0.005
02	0.007	0.024	0.024	0.007	0.140	0.090	0.480	0.480	0.007	0.007	0.007	0.003
03	0.005	0.024	0.024	0.013	0.140	0.090	0.480	0.480	0.007	0.013	0.007	0.005
04	0.005	0.024	0.024	0.013	0.140	0.140	0.480	0.480	0.005	0.013	0.007	0.005
05	0.005	0.050	0.013	0.013	0.140	0.140	0.480	0.480	0.005	0.013	0.007	0.005
06	0.007	0.050	0.013	0.013	0.200	0.140	0.370	0.480	0.005	0.024	0.007	0.005
07	0.013	0.050	0.013	0.013	0.200	0.140	0.480	0.480	0.005	0.024	0.007	0.005
08	0.013	0.050	0.013	0.013	0.200	0.140	0.480	0.480	0.005	0.013	0.007	0.005
09	0.013	0.024	0.013	0.013	0.200	0.140	0.370	0.480	0.005	0.013	0.007	0.007
10	0.013	0.024	0.013	0.013	0.200	0.140	0.370	0.370	0.005	0.013	0.007	0.007
11	0.013	0.024	0.013	0.024	0.200	0.140	0.600	0.285	0.005	0.013	0.007	0.007
12	0.013	0.024	0.013	0.050	0.200	0.140	0.600	0.285	0.007	0.007	0.007	0.007
13	0.024	0.013	0.013	0.050	0.140	0.285	0.600	0.370	0.007	0.007	0.007	0.007
14	0.024	0.013	0.013	0.050	0.140	0.370	0.600	0.285	0.013	0.013	0.007	0.007
15	0.024	0.013	0.013	0.050	0.200	0.370	2.32	0.285	0.013	0.013	0.005	0.007
16	0.024	0.013	0.013	0.050	0.090	0.370	1.43	0.200	0.013	0.013	0.005	0.007
17	0.024	0.024	0.013	0.050	0.050	0.285	0.840	0.200	0.013	0.013	0.003	0.007
18	0.024	0.024	0.013	0.050	0.050	0.285	0.600	0.140	0.013	0.013	0.005	0.007
19	0.024	0.024	0.013	0.050	0.050	0.285	0.480	0.140	0.007	0.013	0.005	0.007
20	0.024	0.720	0.013	0.024	0.050	0.285	0.600	0.090	0.007	0.007	0.005	0.007
21	0.024	0.285	0.013	0.024	0.050	0.370	0.600	0.090	0.007	0.007	0.003	0.050
22	0.024	0.200	0.050	0.024	0.050	0.480	0.600	0.090	0.007	0.007	0.005	0.013
23	0.024	0.200	0.050	0.013	0.050	0.720	0.600	0.090	0.007	0.013	0.003	0.007
24	0.024	0.200	0.050	0.024	0.050	0.720	0.600	0.090	0.007	0.007	0.005	0.003
25	0.024	0.200	0.050	0.024	0.050	0.600	0.600	0.090	0.013	0.007	0.003	0.007
26	0.024	0.200	0.050	0.024	0.090	0.600	0.600	0.090	0.013	0.007	0.005	0.050
27	0.024	0.140	0.050	0.024	0.090	0.840	0.600	0.005	0.013	0.007	0.005	0.050
28	0.024	0.140	0.024	0.024	0.090	0.720	0.600	0.003	0.007	0.007	0.003	0.024
29	0.024	0.090	0.013	0.024	-----	0.600	0.600	0.005	0.007	0.007	0.003	0.024
30	0.024	0.050	0.007	0.090	-----	0.720	0.480	0.005	0.007	0.007	0.003	0.024
31	0.024	-----	0.005	0.140	-----	0.720	-----	0.007	-----	0.007	0.003	-----
Maks.	0.024	2.13	0.050	0.370	0.285	1.59	13.9	0.840	0.013	0.090	0.090	2.70
Min.	0.005	0.013	0.005	0.007	0.050	0.090	0.370	0.003	0.005	0.007	0.003	0.003
Ortalama	0.018	0.098	0.022	0.032	0.121	0.360	0.638	0.243	0.008	0.011	0.005	0.012
LT/SN/Km2	0.882	4.70	1.07	1.55	5.81	17.3	30.6	11.7	0.387	0.518	0.258	0.598
AKIM mm.	2.36	12.2	2.87	4.15	14.0	46.2	79.3	31.2	1.00	1.39	0.692	1.55
MİL. M3	0.049	0.254	0.060	0.086	0.293	0.964	1.65	0.651	0.021	0.029	0.014	0.032

SU YILI (2006) YILLIK TOPLAM AKIM 4.10 MİLYON M3 197 MM. 6.2 LT/SN/Km2

09. Antalya Havzasi

D09A122 SAGARİN D. ÇARDAK

YERİ : **ANTALYA MANAVGAT İSTIKAMETINDE GIDILEREK TAŞAĞILA SAPILIR TAŞAĞILDAN ÇARDAK KÖYÜNE VARILIR. ÇARDAK KÖYÜNDEN DERE YATAGINI SOL SAHILDEN TAKIP EDİLEREK İST. VARILIR. 2.5 METRE EŞELLIDIR.**
31°17'5" Doğu - 36°59'30" Kuzey

YAĞIŞ ALANI : 144,84 km2 **YAKLAŞIK KOT :** 80 m

GÖZLEM SÜRESİ : 01.10.2002 - **30.09.2006**

ORTALAMA AKIMLAR : Gözlem süresinde 3.843 m3/sn. (4 Yıllık) 2006 Su yılında 2.720 m3/sn.

ANLIK EN ÇOK VE EN AZ AKIMLAR:

2006 Su yılında anlık ençok akım	:	**139.**	**m3/sn**	**24.01.2006**
2006 Su yılında anlık enaz akım	:	**0.011**	**m3/sn**	**16.08.2006**
Gözlem süresinde anlık ençok akım	:	**230.**	**m3/sn**	**07.02.2003**
Gözlem süresinde anlık enaz akım	:	**0.010**	**m3/sn**	**23.08.2004**

Akımlar 01 Ekim 2005 'den 30 Eylül 2006' a kadar m3/sn olarak

Gün	Ekim	Kasım	Aralık	Ocak	Şubat	Mart	Nisan	Mayıs	Haziran	Temmuz	Ağustos	Eylül
01	0.054	0.107	1.00	1.64	4.06	4.54	4.06	1.80	0.520	0.256	0.054	0.011
02	0.133	0.107	1.00	1.48	3.28	4.38	3.78	1.80	0.520	0.208	0.054	0.011
03	0.054	0.133	0.880	1.32	2.83	4.38	3.50	1.96	0.520	0.208	0.054	0.011
04	0.054	1.00	0.880	1.32	2.44	4.38	3.50	1.80	0.400	0.208	0.054	0.011
05	0.054	0.520	0.880	1.16	2.28	4.22	3.78	1.64	0.352	0.256	0.054	0.011
06	0.054	0.400	0.760	2.12	3.28	3.78	3.50	1.64	0.352	0.304	0.054	0.011
07	0.054	0.352	0.760	2.12	9.23	3.05	3.28	1.64	0.304	0.256	0.054	0.011
08	0.054	0.304	0.760	1.96	15.8	4.22	3.28	1.48	0.304	0.256	0.054	0.011
09	0.054	0.304	0.760	1.80	16.2	7.34	3.05	1.48	0.304	0.208	0.054	0.011
10	0.054	0.256	0.640	1.64	12.7	6.17	3.05	1.48	0.520	0.208	0.054	0.027
11	0.054	0.256	0.640	1.64	23.0	5.54	3.05	1.32	0.352	0.208	0.054	0.019
12	0.054	0.256	0.640	1.48	50.7	5.54	2.83	1.32	0.304	0.208	0.054	0.019
13	0.133	0.256	0.640	1.48	27.5	5.75	2.60	1.16	0.304	0.208	0.054	0.011
14	0.208	0.256	0.520	1.32	18.6	23.0	2.60	1.00	0.352	0.160	0.054	0.011
15	0.208	0.256	0.880	1.32	14.2	21.5	2.83	1.00	0.304	0.160	0.054	0.011
16	0.256	0.256	0.640	1.16	11.6	16.6	4.22	1.00	0.304	0.160	0.027	0.011
17	0.208	0.256	0.640	1.16	8.96	15.4	3.28	1.00	0.304	0.160	0.011	0.019
18	0.208	1.48	9.23	1.00	8.15	12.3	3.05	0.880	0.304	0.160	0.011	0.019
19	0.208	4.91	18.6	1.16	7.61	10.9	3.05	1.00	0.256	0.160	0.019	0.019
20	0.208	19.8	11.3	1.64	6.59	8.96	2.83	1.00	0.256	0.160	0.080	0.019
21	0.208	8.69	6.17	1.48	6.17	8.15	2.60	0.880	0.256	0.133	0.027	0.019
22	0.208	4.22	4.91	1.32	5.54	7.34	2.60	0.880	0.256	0.107	0.027	0.256
23	0.208	2.60	4.06	1.64	5.12	6.59	2.44	0.760	0.256	0.107	0.011	0.520
24	0.208	1.96	3.28	23.0	4.70	6.17	2.44	0.760	0.256	0.107	0.019	0.520
25	0.160	1.80	2.60	60.2	4.54	5.96	2.28	0.760	0.256	0.107	0.019	1.80
26	0.107	1.48	2.44	23.5	4.38	5.75	2.12	0.640	0.256	0.107	0.019	0.256
27	0.107	1.48	2.12	13.0	4.38	5.33	2.12	0.640	0.256	0.107	0.011	0.133
28	0.107	1.32	1.96	8.96	4.22	4.91	1.96	0.640	0.352	0.107	0.011	0.107
29	0.107	1.16	1.96	6.80	-----	4.54	1.96	0.640	0.400	0.107	0.011	0.107
30	0.107	1.16	1.80	5.54	-----	4.38	1.96	0.520	0.256	0.080	0.011	0.107
31	0.107	-----	1.64	4.54	-----	4.22	-----	0.520	-----	0.080	0.011	-----
Maks.	0.520	33.0	48.6	139.	81.0	35.5	6.59	3.05	3.05	0.352	0.160	14.2
Min.	0.027	0.107	0.520	1.00	2.12	3.05	1.80	0.520	0.208	0.080	0.011	0.011
Ortalama	0.129	1.91	2.74	5.80	10.3	7.59	2.92	1.13	0.331	0.170	0.037	0.137
LT/SN/Km2	0.890	13.2	18.9	40.1	71.0	52.4	20.2	7.80	2.29	1.17	0.253	0.946
AKIM mm.	2.38	34.2	50.7	107.	172.	140.	52.3	20.9	5.93	3.14	0.677	2.45
MİL. M3	0.345	4.95	7.34	15.5	24.9	20.3	7.57	3.03	0.858	0.455	0.098	0.355

SU YILI (2006) YILLIK TOPLAM AKIM 85.70 MİLYON M3 592 MM. 18.8 LT/SN/Km2

09. Antalya Havzasi

D09A123 ÇUKUR Ç. NARLI

YERİ : ISPARTA-ANTALYA YOLUNU TAKİBEN 1.VE 2. TÜNELLERİ GEÇTİKTEN SONRA ISPARTA ÇAYI ILE BİRLEŞEN ÇUKUR ÇAYA VARILIR İSTASYON 1,5 KM İLERİDE SOL SAHİLDEDİR. 30°43'29" Doğu - 37°37'10" Kuzey

YAĞIŞ ALANI : 43,00 km2 YAKLAŞIK KOT : 410 m

GÖZLEM SÜRESİ : 01.10.1999 - 30.09.2006

ORTALAMA AKIMLAR : Gözlem süresinde 0.887 m3/sn. (7 Yıllık) 2006 Su yılında 0.721 m3/sn.

ANLIK EN ÇOK VE EN AZ AKIMLAR:

2006 Su yılında anlık ençok akım	:	5.80	m3/sn	15.03.2006
2006 Su yılında anlık enaz akım	:	0.300	m3/sn	10.10.2005
Gözlem süresinde anlık ençok akım	:	10.9	m3/sn	19.02.2000
Gözlem süresinde anlık enaz akım	:	0.029	m3/sn	23.10.1999

1. Anahtar Eğrisi (Seviyeler cm olarak)

Seviye	Akım	Seviye	Akım	Seviye	Akım	Seviye	Akım
1	0.000	23	0.720	33	1.4	39	1.8
3	0.000	25	0.870	35	1.6	40	1.9
5	0.000	27	1.0	36	1.6	41	2.0
7	0.000	29	1.2	37	1.7	64	3.5
21	0.550	31	1.3	38	1.8	101	6.1

Akımlar 01 Ekim 2005 'den 30 Eylül 2006' a kadar m3/sn olarak

Gün	Ekim	Kasım	Aralık	Ocak	Şubat	Mart	Nisan	Mayıs	Haziran	Temmuz	Ağustos	Eylül
01	0.780	0.300	0.300	0.340	1.06	1.20	1.68	0.710	0.640	0.570	0.380	0.380
02	0.640	0.300	0.300	0.340	1.06	1.36	1.60	0.710	0.640	0.570	0.380	0.380
03	0.640	0.300	0.300	0.340	1.20	1.36	1.52	0.710	0.640	0.570	0.380	0.380
04	0.500	0.300	0.300	0.340	1.20	1.60	1.44	0.710	0.640	0.570	0.380	0.380
05	0.460	0.300	0.300	0.340	1.20	1.84	1.36	0.780	0.640	0.500	0.380	0.380
06	0.420	0.300	0.300	0.340	1.36	1.92	1.36	0.780	0.640	0.500	0.380	0.420
07	0.420	0.300	0.300	0.340	1.36	1.92	1.36	0.850	0.640	0.500	0.380	0.460
08	0.340	0.300	0.300	0.340	1.52	1.92	1.28	0.850	0.640	0.500	0.380	0.570
09	0.340	0.300	0.300	0.340	1.52	1.92	1.28	0.780	0.640	0.500	0.380	0.500
10	0.300	0.300	0.300	0.340	1.52	1.92	1.20	0.780	0.640	0.500	0.380	0.500
11	0.300	0.300	0.300	0.340	1.52	2.00	1.20	0.710	0.640	0.500	0.380	0.500
12	0.300	0.300	0.300	0.340	1.52	2.00	1.20	0.710	0.570	0.500	0.380	0.500
13	0.300	0.300	0.300	0.340	1.60	2.00	1.13	0.710	0.570	0.420	0.380	0.500
14	0.300	0.300	0.300	0.340	1.60	4.40	1.13	0.710	0.570	0.420	0.380	0.420
15	0.300	0.300	0.300	0.340	1.60	5.80	1.13	0.710	0.570	0.420	0.380	0.420
16	0.300	0.300	0.340	0.340	1.36	3.00	1.13	0.710	0.570	0.420	0.380	0.420
17	0.300	0.300	0.340	0.340	1.36	2.10	1.13	0.710	0.570	0.420	0.380	0.420
18	0.300	0.300	0.340	0.420	1.36	2.00	1.13	0.710	0.570	0.420	0.380	0.420
19	0.300	0.300	0.340	0.420	1.36	1.84	1.13	0.710	0.570	0.420	0.380	0.380
20	0.300	0.300	0.340	0.640	1.36	1.84	1.06	0.710	0.570	0.420	0.460	0.380
21	0.300	0.300	0.340	0.640	1.28	1.84	1.06	0.710	0.570	0.420	0.640	0.380
22	0.300	0.300	0.340	0.640	1.28	1.84	1.06	0.710	0.570	0.420	0.570	0.380
23	0.300	0.300	0.340	0.780	1.28	1.84	1.06	0.710	0.570	0.380	0.420	0.380
24	0.300	0.300	0.340	1.06	1.28	1.84	1.06	0.710	0.570	0.380	0.420	0.380
25	0.300	0.300	0.340	1.06	1.28	1.84	0.990	0.710	0.570	0.380	0.420	0.380
26	0.300	0.300	0.340	1.06	1.28	1.84	0.990	0.710	0.570	0.380	0.420	0.380
27	0.300	0.300	0.340	1.06	1.20	1.76	0.920	0.640	0.570	0.380	0.380	0.380
28	0.300	0.300	0.340	1.06	1.20	1.76	0.850	0.640	0.570	0.380	0.380	0.380
29	0.300	0.300	0.340	1.06	-----	1.76	0.780	0.640	0.570	0.380	0.380	0.380
30	0.300	0.300	0.340	1.06	-----	1.68	0.780	0.640	0.570	0.380	0.380	0.380
31	0.300	-----	0.340	1.06	-----	1.68	-----	0.640	-----	0.380	0.380	-----
Maks.	0.780	0.300	0.340	1.06	1.60	5.80	1.68	0.850	0.640	0.570	0.640	0.570
Min.	0.300	0.300	0.300	0.340	1.06	1.20	0.780	0.640	0.570	0.380	0.380	0.380
Ortalama	0.359	0.300	0.321	0.574	1.35	2.05	1.17	0.717	0.596	0.448	0.402	0.417
LT/SN/Km2	8.36	6.98	7.46	13.4	31.3	47.7	27.1	16.7	13.9	10.4	9.35	9.70
AKIM mm.	22.4	18.1	20.0	35.8	75.8	128.	70.3	44.6	35.9	27.9	25.1	25.1
MİL. M3	0.962	0.778	0.859	1.54	3.26	5.50	3.02	1.92	1.54	1.20	1.08	1.08

SU YILI (2006) YILLIK TOPLAM AKIM 22.74 MİLYON M3 529 MM. 16.8 LT/SN/Km2

09. Antalya Havzasi

D09A124 KOCA D. AKBAS

YERİ : **ANTALYA-SERİK YOLUNDAN SERIK DENIZTEPE TAKIBEN 17 KM SONRA ZEYTINTAŞI KAVŞAĞINDAN 5 KM SONRA AKBAŞ KÖYÜNDE SOL SAHILDEDİR. 30°5'3" Doğu - 37°6'0" Kuzey**

YAĞIŞ ALANI : **42,60 km2** **YAKLAŞIK KOT : 147 m**

GÖZLEM SÜRESİ : **01.10.2003 - 30.09.2006**

ORTALAMA AKIMLAR : **Gözlem süresinde 0.828 m3/sn. (3 Yıllık) 2006 Su yılında 0.784 m3/sn.**

ANLIK EN ÇOK VE EN AZ AKIMLAR:

2006 Su yılında anlık ençok akım	**:**	**34.4**	**m3/sn**	**24.01.2006**
2006 Su yılında anlık enaz akım	**:**	**0.003**	**m3/sn**	**01.10.2005**
Gözlem süresinde anlık ençok akım	**:**	**36.2**	**m3/sn**	**21.04.2004**
Gözlem süresinde anlık enaz akım	**:**	**0.000**	**m3/sn**	**01.11.2004**

Akımlar 01 Ekim 2005 'den 30 Eylül 2006' a kadar m3/sn olarak

Gün	Ekim	Kasım	Aralık	Ocak	Şubat	Mart	Nisan	Mayıs	Haziran	Temmuz	Ağustos	Eylül
01	0.003	0.003	0.165	0.474	1.95	1.47	1.63	0.410	0.110	0.110	0.013	0.005
02	0.003	0.003	0.165	0.411	1.79	1.47	1.63	0.410	0.110	0.064	0.013	0.005
03	0.003	0.006	0.125	0.348	1.47	1.47	1.47	0.410	0.110	0.064	0.013	0.005
04	0.003	0.009	0.125	0.348	1.47	1.63	1.47	0.410	0.110	0.064	0.013	0.005
05	0.003	0.006	0.125	0.348	1.47	1.47	1.63	0.328	0.110	0.087	0.013	0.005
06	0.003	0.006	0.065	1.30	2.28	1.47	1.63	0.328	0.110	0.087	0.013	0.003
07	0.003	0.006	0.065	1.40	3.80	1.30	1.63	0.328	0.110	0.064	0.013	0.003
08	0.003	0.006	0.047	1.20	6.40	1.63	1.47	0.247	0.110	0.064	0.013	0.003
09	0.003	0.006	0.047	0.900	4.76	2.84	1.30	0.247	0.110	0.046	0.013	0.003
10	0.003	0.006	0.047	0.900	4.28	2.11	1.30	0.247	0.110	0.046	0.013	0.003
11	0.003	0.006	0.047	0.900	4.52	2.28	0.980	0.247	0.110	0.046	0.009	0.003
12	0.003	0.006	0.047	0.700	4.76	2.60	0.980	0.247	0.110	0.030	0.009	0.003
13	0.003	0.006	0.047	0.600	4.52	3.32	0.817	0.247	0.110	0.030	0.009	0.005
14	0.003	0.006	0.047	0.600	4.04	9.75	0.817	0.165	0.110	0.030	0.009	0.005
15	0.003	0.006	0.047	0.537	3.32	6.40	0.817	0.165	0.110	0.030	0.009	0.005
16	0.003	0.009	0.047	0.537	2.44	5.28	0.817	0.165	0.110	0.030	0.009	0.005
17	0.003	0.009	0.047	0.474	2.28	4.76	0.817	0.165	0.110	0.030	0.009	0.005
18	0.003	0.165	2.68	0.474	2.28	4.28	0.817	0.165	0.087	0.030	0.009	0.005
19	0.003	0.205	5.00	0.474	1.79	3.80	0.736	0.165	0.087	0.030	0.009	0.005
20	0.003	1.00	2.80	0.348	1.79	3.32	0.736	0.165	0.087	0.030	0.009	0.005
21	0.003	0.411	2.08	0.348	1.30	2.84	0.736	0.165	0.087	0.019	0.005	0.005
22	0.003	0.348	1.50	0.348	1.30	2.60	0.736	0.165	0.087	0.019	0.005	0.005
23	0.003	0.285	1.30	0.474	1.47	2.60	0.654	0.138	0.110	0.019	0.005	0.005
24	0.003	0.285	1.10	8.58	1.47	2.28	0.573	0.138	0.110	0.019	0.005	0.005
25	0.003	0.285	1.00	13.7	1.47	2.44	0.573	0.138	0.110	0.019	0.005	0.005
26	0.003	0.245	0.700	6.68	1.47	2.11	0.573	0.138	0.110	0.013	0.005	0.005
27	0.003	0.205	0.700	4.76	1.47	2.11	0.573	0.138	0.064	0.013	0.003	0.005
28	0.003	0.165	0.537	3.80	1.47	1.95	0.491	0.138	0.110	0.013	0.003	0.005
29	0.003	0.165	0.537	2.84	-----	1.79	0.491	0.138	0.110	0.013	0.003	0.005
30	0.003	0.165	0.474	2.44	-----	1.63	0.491	0.138	0.110	0.013	0.005	0.005
31	0.003	-----	0.474	2.11	-----	1.63	-----	0.110	-----	0.013	0.005	-----
Maks.	0.003	2.68	20.9	34.4	10.1	19.1	2.44	0.491	0.247	0.328	0.013	0.005
Min.	0.003	0.003	0.047	0.348	0.736	1.30	0.491	0.110	0.064	0.013	0.003	0.003
Ortalama	0.003	0.134	0.716	1.91	2.60	2.79	0.980	0.220	0.105	0.038	0.009	0.005
LT/SN/Km2	0.070	3.16	16.8	44.9	61.1	65.6	23.0	5.15	2.46	0.897	0.204	0.106
AKIM mm.	0.189	8.18	45.0	120.	148.	176.	59.6	13.8	6.37	2.40	0.546	0.276
MİL. M3	0.008	0.349	1.92	5.13	6.29	7.48	2.54	0.588	0.271	0.102	0.023	0.012

SU YILI (2006) YILLIK TOPLAM AKIM 24.71 MİLYON M3 580 MM. 18.4 LT/SN/Km2

09. Antalya Havzasi

D09A125 KURUPİNAR D. KÜÇÜKKÖY

YERİ : **ANTALYA KORKUTELİ ISTIKAMETINDE GIDILEREK KORKUTELIYE VARILIR KORKUTELI BOZOVA ISTIKAMETINDE GIDILEREK KÜÇÜKKÖY YOL AYRIMINA VARILIR. YAKLAŞIK 7 KM SONRA KÜÇÜKKÖYE VARILIR. 30°18'13" Doğu - 37°6'47" Kuzey**

YAĞIŞ ALANI : 11,60 km2 **YAKLAŞIK KOT :** 890 m

GÖZLEM SÜRESİ : 01.10.2004 - **30.09.2006**

ORTALAMA AKIMLAR : **Gözlem süresinde** 0.013 m3/sn. (2 Yıllık) 2006 Su yılında 0.012 m3/sn.

ANLIK EN ÇOK VE EN AZ AKIMLAR:

2006 Su yılında anlık ençok akım	:	**4.36**	m3/sn	**14.06.2006**
2006 Su yılında anlık enaz akım	:	**0.000**	m3/sn	**09.06.2006**
Gözlem süresinde anlık ençok akım	:	**7.28**	m3/sn	**24.09.2005**
Gözlem süresinde anlık enaz akım	:	**0.000**	m3/sn	**08.08.2005**

Akımlar 01 Ekim 2005 'den 30 Eylül 2006' a kadar m3/sn olarak

Gün	Ekim	Kasım	Aralık	Ocak	Şubat	Mart	Nisan	Mayıs	Haziran	Temmuz	Ağustos	Eylül
01	0.011	0.011	0.011	0.011	0.011	0.012	0.003	0.011	0.092	KURU	0.003	KURU
02	0.011	0.011	0.011	0.011	0.011	0.012	0.003	0.012	0.047	KURU	0.002	KURU
03	0.011	0.012	0.011	0.011	0.011	0.012	0.003	0.012	0.003	KURU	0.002	KURU
04	0.011	0.011	0.011	0.011	0.011	0.012	0.003	0.017	KURU	0.001	0.002	KURU
05	0.011	0.011	0.011	0.011	0.011	0.012	0.017	0.017	KURU	0.003	0.002	KURU
06	0.011	0.011	0.011	0.011	0.012	0.012	0.017	0.017	KURU	0.002	0.002	KURU
07	0.011	0.011	0.011	0.011	0.012	0.012	0.017	0.017	KURU	0.002	KURU	KURU
08	0.011	0.011	0.011	0.011	0.031	0.012	0.017	0.031	KURU	0.002	KURU	KURU
09	0.011	0.011	0.011	0.011	0.017	0.012	0.017	0.031	KURU	0.002	KURU	KURU
10	0.011	0.011	0.011	0.011	0.012	0.012	0.017	0.031	0.001	0.002	KURU	KURU
11	0.011	0.011	0.011	0.011	0.012	0.012	0.017	0.047	KURU	0.002	KURU	KURU
12	0.011	0.011	0.011	0.011	0.012	0.012	0.017	0.047	KURU	0.002	KURU	KURU
13	0.011	0.011	0.011	0.011	0.012	0.062	0.017	0.047	0.001	0.002	KURU	KURU
14	0.011	0.011	0.011	0.011	0.012	0.062	0.017	0.047	0.011	0.002	KURU	KURU
15	0.011	0.011	0.011	0.011	0.012	0.017	0.031	0.062	0.001	0.002	KURU	KURU
16	0.011	0.011	0.011	0.011	0.012	0.017	0.012	0.062	0.001	0.002	KURU	KURU
17	0.011	0.011	0.011	0.011	0.012	0.017	0.012	0.062	KURU	0.002	KURU	KURU
18	0.011	0.011	0.011	0.011	0.012	0.017	0.012	0.062	KURU	0.002	KURU	KURU
19	0.011	0.017	0.011	0.003	0.012	0.017	0.012	0.062	0.001	0.002	KURU	KURU
20	0.011	0.012	0.011	0.003	0.012	0.017	0.012	0.062	0.001	0.003	KURU	KURU
21	0.011	0.011	0.011	0.003	0.012	0.017	0.012	0.076	KURU	0.003	KURU	KURU
22	0.011	0.011	0.011	0.003	0.012	0.017	0.031	0.076	KURU	0.003	KURU	KURU
23	0.011	0.011	0.011	0.003	0.012	0.017	0.012	0.076	KURU	0.003	KURU	KURU
24	0.011	0.011	0.011	0.003	0.012	0.017	0.011	0.076	KURU	0.003	KURU	KURU
25	0.011	0.011	0.011	0.012	0.012	0.017	0.011	0.076	KURU	0.003	KURU	KURU
26	0.011	0.011	0.011	0.011	0.012	0.017	0.011	0.076	KURU	0.003	KURU	KURU
27	0.011	0.011	0.011	0.011	0.012	0.017	0.011	0.092	0.003	0.003	KURU	KURU
28	0.011	0.011	0.011	0.011	0.012	0.017	0.011	0.092	0.002	0.003	KURU	KURU
29	0.011	0.011	0.011	0.011	-----	0.017	0.011	0.092	0.001	0.003	KURU	KURU
30	0.011	0.011	0.011	0.011	-----	0.003	0.011	0.092	KURU	0.003	KURU	KURU
31	0.011	-----	0.011	0.011	-----	0.003	-----	0.092	-----	0.003	KURU	-----
Maks.	0.430	2.46	0.012	0.047	0.160	1.66	1.40	0.092	4.36	0.716	0.003	KURU
Min.	0.003	0.003	0.003	0.003	0.011	0.003	0.003	0.011	KURU	KURU	KURU	KURU
Ortalama	0.011	0.011	0.011	0.009	0.013	0.017	0.014	0.054	0.006	0.002	0.000	KURU
LT/SN/Km2	0.948	0.971	0.948	0.818	1.09	1.47	1.16	4.65	0.474	0.189	0.036	0.000
AKIM mm.	2.54	2.52	2.54	2.19	2.64	3.94	3.02	12.5	1.23	0.506	0.097	0.000
MİL. M3	0.029	0.029	0.029	0.025	0.031	0.046	0.035	0.144	0.014	0.006	0.001	0.000

SU YILI (2006) YILLIK TOPLAM AKIM 0.39 MİLYON M3 34 MM. 1.1 LT/SN/Km2

09. Antalya Havzasi

D09A126 ASAR D. KÜÇÜKKÖY

YERİ : **ANTALYA-KORKUTELİ-BOZOVA ISTIKAMETINDE KÜÇÜKKÖY YOL AYRIMINDAN 7 KM SONRA KÜÇÜKKÖYE VARILIR. KÖYÜN 2 KM KUZEYINDEDIR. 30°17'43" Doğu - 37°8'12" Kuzey**

YAĞIŞ ALANI : 5,80 km2 **YAKLAŞIK KOT :** 910 m

GÖZLEM SÜRESİ : 01.10.2004 - **30.09.2006**

ORTALAMA AKIMLAR : Gözlem süresinde 0.020 m3/sn. (2 Yıllık) 2006 Su yılında 0.022 m3/sn.

ANLIK EN ÇOK VE EN AZ AKIMLAR:

2006 Su yılında anlık ençok akım	:	**0.880 m3/sn**	**09.06.2006**
2006 Su yılında anlık enaz akım	:	**0.005 m3/sn**	**01.10.2005**
Gözlem süresinde anlık ençok akım	:	**0.880 m3/sn**	**09.06.2006**
Gözlem süresinde anlık enaz akım	:	**0.005 m3/sn**	**01.10.2005**

Akımlar 01 Ekim 2005 'den 30 Eylül 2006' a kadar m3/sn olarak

Gün	Ekim	Kasım	Aralık	Ocak	Şubat	Mart	Nisan	Mayıs	Haziran	Temmuz	Ağustos	Eylül
01	0.016	0.021	0.021	0.021	0.021	0.019	0.019	0.025	0.021	0.028	0.028	0.021
02	0.012	0.021	0.021	0.021	0.021	0.021	0.019	0.021	0.021	0.028	0.028	0.021
03	0.013	0.021	0.021	0.021	0.021	0.021	0.019	0.021	0.021	0.028	0.028	0.021
04	0.016	0.021	0.021	0.021	0.021	0.021	0.019	0.021	0.021	0.028	0.028	0.021
05	0.016	0.021	0.021	0.021	0.021	0.021	0.019	0.021	0.021	0.028	0.028	0.021
06	0.016	0.021	0.021	0.021	0.021	0.021	0.019	0.021	0.021	0.028	0.021	0.021
07	0.016	0.021	0.021	0.021	0.021	0.021	0.019	0.021	0.021	0.028	0.021	0.028
08	0.016	0.021	0.021	0.021	0.028	0.021	0.019	0.021	0.021	0.028	0.021	0.028
09	0.016	0.021	0.021	0.021	0.025	0.021	0.019	0.021	0.028	0.028	0.021	0.028
10	0.013	0.021	0.021	0.021	0.021	0.021	0.021	0.021	0.035	0.028	0.021	0.028
11	0.013	0.021	0.021	0.021	0.021	0.021	0.021	0.021	0.035	0.028	0.021	0.028
12	0.013	0.021	0.021	0.021	0.021	0.021	0.021	0.021	0.035	0.028	0.021	0.028
13	0.013	0.021	0.021	0.021	0.021	0.025	0.021	0.021	0.035	0.028	0.021	0.028
14	0.013	0.021	0.021	0.021	0.021	0.028	0.021	0.021	0.042	0.028	0.021	0.028
15	0.013	0.021	0.021	0.021	0.021	0.021	0.025	0.021	0.032	0.028	0.021	0.028
16	0.013	0.021	0.021	0.021	0.019	0.021	0.021	0.021	0.032	0.028	0.021	0.028
17	0.013	0.021	0.021	0.021	0.019	0.021	0.021	0.021	0.032	0.028	0.021	0.028
18	0.013	0.025	0.021	0.021	0.021	0.021	0.021	0.021	0.032	0.028	0.021	0.028
19	0.013	0.025	0.021	0.021	0.021	0.021	0.019	0.021	0.032	0.028	0.021	0.028
20	0.013	0.025	0.021	0.021	0.021	0.021	0.019	0.021	0.032	0.028	0.021	0.028
21	0.013	0.025	0.021	0.021	0.021	0.021	0.019	0.021	0.032	0.028	0.021	0.028
22	0.013	0.021	0.021	0.021	0.021	0.021	0.028	0.021	0.028	0.028	0.021	0.028
23	0.013	0.021	0.021	0.021	0.021	0.021	0.025	0.021	0.028	0.028	0.021	0.028
24	0.013	0.021	0.021	0.021	0.021	0.021	0.021	0.021	0.028	0.028	0.021	0.028
25	0.016	0.021	0.021	0.021	0.021	0.021	0.021	0.021	0.028	0.028	0.021	0.028
26	0.016	0.021	0.021	0.021	0.021	0.019	0.021	0.021	0.028	0.028	0.021	0.028
27	0.016	0.021	0.021	0.021	0.021	0.019	0.021	0.021	0.028	0.028	0.021	0.028
28	0.016	0.021	0.021	0.021	0.019	0.021	0.021	0.021	0.028	0.028	0.021	0.028
29	0.016	0.021	0.021	0.021	-----	0.019	0.021	0.021	0.028	0.028	0.021	0.028
30	0.021	0.021	0.021	0.021	-----	0.019	0.021	0.021	0.028	0.028	0.021	0.028
31	0.021	-----	0.021	0.021	-----	0.019	-----	0.021	-----	0.028	0.021	-----
Maks.	0.021	0.048	0.021	0.021	0.032	0.048	0.250	0.048	0.880	0.028	0.028	0.028
Min.	0.005	0.019	0.019	0.016	0.016	0.016	0.016	0.019	0.019	0.021	0.021	0.021
Ortalama	0.015	0.022	0.021	0.021	0.021	0.021	0.021	0.021	0.028	0.028	0.022	0.027
LT/SN/Km2	2.53	3.71	3.62	3.62	3.65	3.62	3.57	3.64	4.91	4.83	3.82	4.59
AKIM mm.	6.76	9.62	9.70	9.70	8.83	9.68	9.25	9.76	12.7	12.9	10.2	11.9
MİL. M3	0.039	0.056	0.056	0.056	0.051	0.056	0.054	0.057	0.074	0.075	0.059	0.069

SU YILI (2006) YILLIK TOPLAM AKIM 0.70 MİLYON M3 121 MM. 3.8 LT/SN/Km2

09. Antalya Havzasi

D09A127 DELİCE Ç. YENİKÖY

YERİ : **ANTALYA-ALANYA-KONAKLI İSTIKAMETINDE GÜZELBAĞ YOLU TAKIP EDILEREK 7 KM SONRA YENIKÖYE VARILIR. KÖYÜN IÇINDEN SOLA SAPILIR 2 KM SONRA İSTASYONA VARILIR. 31°57'40" Doğu - 36°37'56" Kuzey**

YAĞIŞ ALANI : **45,00 km2** **YAKLAŞIK KOT : 210 m**

GÖZLEM SÜRESİ : **01.10.2005 - 30.09.2006**

ORTALAMA AKIMLAR : **Gözlem süresinde 0.366 m3/sn. (1 Yıllık) 2006 Su yılında 0.366 m3/sn.**

ANLIK EN ÇOK VE EN AZ AKIMLAR:

2006 Su yılında anlık ençok akım	:	**9.91**	**m3/sn**	**08.02.2006**
2006 Su yılında anlık enaz akım	:	**0.001**	**m3/sn**	**01.10.2005**
Gözlem süresinde anlık ençok akım	:	**9.91**	**m3/sn**	**08.02.2006**
Gözlem süresinde anlık enaz akım	:	**0.001**	**m3/sn**	**01.10.2005**

Akımlar 01 Ekim 2005 'den 30 Eylül 2006' a kadar m3/sn olarak

Gün	Ekim	Kasım	Aralık	Ocak	Şubat	Mart	Nisan	Mayıs	Haziran	Temmuz	Ağustos	Eylül
01	0.001	0.011	0.048	0.134	0.335	0.415	0.920	0.230	0.063	0.032	0.011	0.025
02	0.002	0.018	0.048	0.110	0.265	0.370	0.864	0.230	0.079	0.025	0.011	0.025
03	0.002	0.018	0.048	0.110	0.265	0.370	0.808	0.230	0.063	0.025	0.018	0.025
04	0.002	0.206	0.048	0.110	0.206	0.335	0.976	0.206	0.063	0.025	0.009	0.025
05	0.002	0.025	0.032	0.110	0.206	0.370	0.808	0.206	0.048	0.032	0.009	0.025
06	0.002	0.018	0.032	0.110	0.550	0.335	0.696	0.206	0.048	0.032	0.009	0.025
07	0.002	0.018	0.032	0.110	5.56	0.300	0.640	0.206	0.048	0.032	0.009	0.025
08	0.002	0.018	0.032	0.110	6.00	0.976	0.640	0.206	0.048	0.025	0.009	0.025
09	0.002	0.018	0.032	0.110	3.77	2.20	0.595	0.182	0.048	0.025	0.009	0.025
10	0.002	0.011	0.032	0.110	3.14	1.26	0.550	0.206	0.048	0.025	0.011	0.025
11	0.002	0.011	0.032	0.110	3.14	1.03	0.550	0.158	0.048	0.025	0.011	0.032
12	0.002	0.011	0.025	0.110	4.55	0.920	0.505	0.158	0.048	0.025	0.009	0.025
13	0.002	0.011	0.025	0.110	4.22	1.32	0.460	0.158	0.048	0.025	0.009	0.025
14	0.002	0.011	0.025	0.110	2.87	2.69	0.460	0.158	0.048	0.025	0.011	0.025
15	0.002	0.011	0.048	0.110	2.12	3.14	0.505	0.134	0.048	0.025	0.011	0.025
16	0.002	0.011	0.134	0.094	1.62	2.36	0.505	0.134	0.048	0.025	0.011	0.032
17	0.002	0.011	0.230	0.094	1.32	1.96	0.415	0.158	0.032	0.025	0.009	0.025
18	0.002	0.158	0.640	0.094	1.14	1.80	0.370	0.134	0.032	0.025	0.009	0.018
19	0.004	0.158	2.12	0.300	0.976	2.28	0.335	0.158	0.025	0.025	0.011	0.025
20	0.004	0.265	0.752	0.415	0.864	1.88	0.335	0.134	0.032	0.011	0.011	0.025
21	0.004	0.079	0.265	0.265	0.752	1.68	0.335	0.134	0.032	0.011	0.018	0.025
22	0.002	0.063	0.182	0.206	0.640	1.44	0.335	0.110	0.032	0.011	0.018	0.032
23	0.002	0.063	0.134	0.230	0.640	1.26	0.335	0.110	0.032	0.011	0.018	0.048
24	0.009	0.048	0.134	0.265	0.550	1.38	0.335	0.110	0.032	0.011	0.018	0.048
25	0.004	0.063	0.134	4.31	0.505	1.74	0.335	0.079	0.032	0.011	0.018	0.025
26	0.004	0.063	0.134	2.69	0.505	1.50	0.335	0.079	0.032	0.011	0.018	0.011
27	0.004	0.048	0.134	1.20	0.460	1.38	0.300	0.079	0.032	0.011	0.018	0.009
28	0.004	0.048	0.134	0.808	0.415	1.26	0.335	0.079	0.032	0.011	0.018	0.009
29	0.004	0.048	0.134	0.595	-----	1.14	0.300	0.079	0.032	0.011	0.025	0.011
30	0.004	0.048	0.134	0.505	-----	1.03	0.300	0.079	0.032	0.011	0.025	0.011
31	0.009	-----	0.134	0.415	-----	0.976	-----	0.079	-----	0.011	0.025	-----
Maks.	0.032	1.14	3.77	9.19	9.91	6.43	3.32	0.230	0.079	0.032	0.025	0.370
Min.	0.001	0.009	0.025	0.094	0.206	0.300	0.206	0.079	0.025	0.009	0.009	0.009
Ortalama	0.003	0.053	0.196	0.457	1.70	1.33	0.506	0.149	0.043	0.020	0.014	0.025
LT/SN/Km2	0.067	1.18	4.35	10.2	37.8	29.5	11.2	3.30	0.952	0.455	0.305	0.545
AKIM mm.	0.179	3.05	11.7	27.2	91.4	78.9	29.1	8.85	2.47	1.22	0.818	1.41
MİL. M3	0.008	0.137	0.524	1.22	4.11	3.55	1.31	0.398	0.111	0.055	0.037	0.064

SU YILI (2006) YILLIK TOPLAM AKIM 11.52 MİLYON M3 256 MM. 8.1 LT/SN/Km2

10

BURDUR GÖLÜ KAPALI HAVZASI

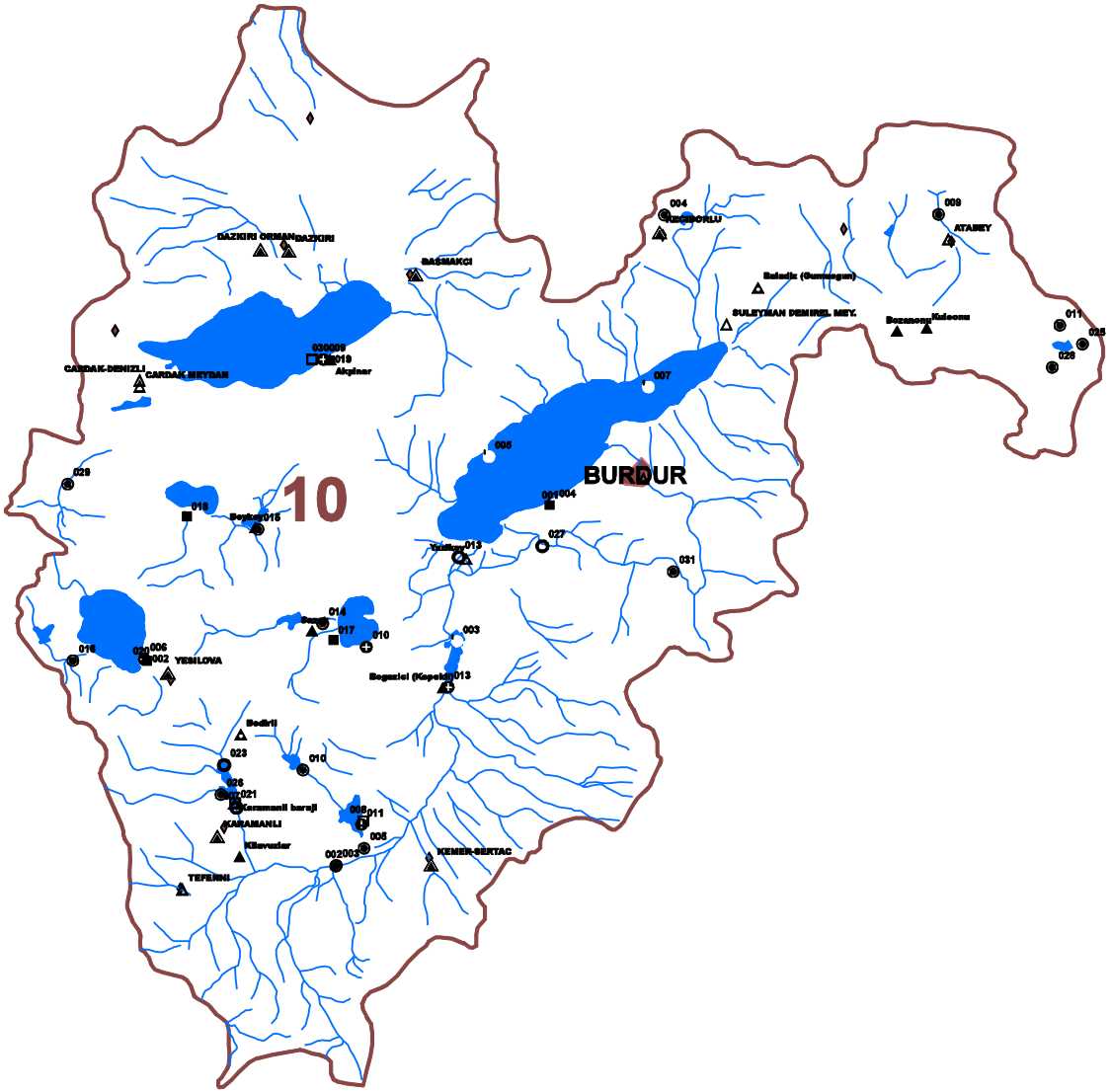

10. BURDUR GÖLLER HAVZASI

- DSI-AGI(Açik)
- DSI-AGI(Kapali)
- DSI-GGI(Açik)
- DSI-GGI(Kapali)
- DSI-MGI(Açik)
- DSI-MGI(Kapali)
- EIE-AGI(Açik)
- EIE-AGI(Kapali)
- DMI-MGI(Açik)
- DMI-MGI(Kapali)

N

1:500.000

10. Burdur Göller Havzasi

D10A013 BOZÇAY YAZİKÖY

YERİ : **BURDUR TEFENNİ YOLUNUN 18.KM.SİNDEN SAGA AYRILAN YOLUN 6 KM SİNDEKİ YAZIKÖY KÖPRÜSÜNDEDİR**
HARİTA PAFTA NO: M24-D1
30°4'55" Doğu - 37°38'15" Kuzey

YAĞIŞ ALANI : **1571,30 km2** **YAKLAŞIK KOT : 865 m**

GÖZLEM SÜRESİ : **10.04.1968 - 30.09.2006**

ORTALAMA AKIMLAR : **Gözlem süresinde 1.370 m3/sn. (31 Yıllık) 2006 Su yılında 0.182 m3/sn.**

ANLIK EN ÇOK VE EN AZ AKIMLAR:

2006 Su yılında anlık ençok akım	:	**0.860**	**m3/sn**	**13.02.2006**
2006 Su yılında anlık enaz akım	:	**0.000**	**m3/sn**	**06.08.2006**
Gözlem süresinde anlık ençok akım	:	**40.0**	**m3/sn**	**15.01.1969**
Gözlem süresinde anlık enaz akım	:	**0.000**	**m3/sn**	**06.08.1974**

15. Anahtar Eğrisi (Seviyeler cm olarak)

Seviye	Akım	Seviye	Akım	Seviye	Akım	Seviye	Akım
5	0.000	20	0.160	40	1.4	90	5.2
8	0.012	23	0.270	50	2.2	100	6.0
11	0.028	26	0.420	60	2.9	110	6.7
14	0.054	30	0.660	70	3.7	120	7.5
17	0.096	33	0.852	80	4.4	130	8.1

Akımlar 01 Ekim 2005 'den 30 Eylül 2006' a kadar m3/sn olarak

Gün	Ekim	Kasım	Aralık	Ocak	Şubat	Mart	Nisan	Mayıs	Haziran	Temmuz	Ağustos	Eylül
01	0.013	0.023	0.460	0.320	0.280	0.400	0.400	0.160	0.010	0.030	0.002	KURU
02	0.016	0.032	0.360	0.320	0.240	0.460	0.360	0.280	0.010	0.030	0.002	KURU
03	0.016	0.052	0.360	0.320	0.240	0.460	0.320	0.160	0.016	0.030	0.002	KURU
04	0.016	0.240	0.360	0.320	0.240	0.460	0.280	0.120	0.010	0.030	KURU	KURU
05	0.032	0.280	0.320	0.320	0.240	0.460	0.240	0.120	0.006	0.030	KURU	KURU
06	0.052	0.320	0.320	0.320	0.240	0.460	0.160	0.120	0.006	0.030	KURU	KURU
07	0.060	0.320	0.320	0.320	0.240	0.460	0.120	0.120	0.006	0.030	KURU	KURU
08	0.060	0.280	0.320	0.320	0.280	0.460	0.110	0.120	0.006	0.030	KURU	KURU
09	0.060	0.400	0.320	0.320	0.280	0.460	0.090	0.120	0.006	0.030	KURU	KURU
10	0.060	0.520	0.320	0.320	0.360	0.460	0.090	0.120	0.006	0.016	KURU	KURU
11	0.060	0.460	0.280	0.320	0.460	0.460	0.090	0.090	0.022	0.016	KURU	KURU
12	0.060	0.360	0.240	0.320	0.460	0.460	0.110	0.090	0.016	0.016	KURU	KURU
13	0.060	0.240	0.240	0.240	0.860	0.520	0.090	0.200	0.022	0.016	KURU	KURU
14	0.060	0.240	0.240	0.360	0.780	0.700	0.070	0.240	0.040	0.016	KURU	KURU
15	0.060	0.240	0.240	0.360	0.640	0.700	0.070	0.200	0.040	0.016	KURU	0.002
16	0.060	0.240	0.240	0.360	0.460	0.640	0.090	0.200	0.040	0.016	KURU	0.002
17	0.060	0.280	0.240	0.360	0.400	0.640	0.110	0.110	0.040	0.016	KURU	0.002
18	0.060	0.280	0.240	0.320	0.360	0.640	0.110	0.070	0.040	0.016	KURU	0.002
19	0.060	0.320	0.240	0.320	0.360	0.580	0.110	0.070	0.040	0.016	KURU	0.002
20	0.060	0.400	0.280	0.280	0.360	0.580	0.090	0.070	0.040	0.016	KURU	0.002
21	0.060	0.520	0.280	0.280	0.360	0.580	0.090	0.070	0.040	0.016	KURU	0.002
22	0.060	0.460	0.280	0.280	0.360	0.580	0.090	0.070	0.040	0.010	KURU	0.002
23	0.060	0.460	0.280	0.280	0.360	0.580	0.110	0.058	0.040	0.010	KURU	0.002
24	0.060	0.460	0.280	0.280	0.360	0.580	0.200	0.058	0.040	0.010	KURU	KURU
25	0.060	0.460	0.360	0.280	0.320	0.580	0.160	0.040	0.040	0.010	KURU	0.040
26	0.060	0.460	0.400	0.280	0.320	0.460	0.160	0.040	0.040	0.006	KURU	0.010
27	0.060	0.460	0.320	0.280	0.320	0.400	0.160	0.030	0.058	0.004	KURU	0.090
28	0.052	0.460	0.320	0.280	0.360	0.400	0.160	0.022	0.058	0.004	KURU	0.040
29	0.032	0.460	0.320	0.280	-----	0.400	0.160	0.022	0.058	0.004	KURU	0.058
30	0.023	0.400	0.320	0.280	-----	0.400	0.120	0.022	0.030	0.002	KURU	0.030
31	0.023	-----	0.320	0.160	-----	0.400	-----	0.022	-----	0.002	KURU	-----
Maks.	0.060	0.520	0.460	0.360	0.860	0.700	0.400	0.280	0.058	0.030	0.002	0.090
Min.	0.013	0.023	0.240	0.160	0.240	0.400	0.070	0.022	0.006	0.002	KURU	KURU
Ortalama	0.050	0.338	0.304	0.303	0.376	0.510	0.151	0.104	0.029	0.017	0.000	0.010
LT/SN/Km2	0.032	0.215	0.193	0.193	0.240	0.325	0.096	0.066	0.018	0.011	0.000	0.006
AKIM mm.	0.084	0.557	0.518	0.517	0.580	0.870	0.249	0.178	0.048	0.029	0.000	0.016
MİL. M3	0.133	0.875	0.814	0.812	0.911	1.37	0.391	0.279	0.075	0.045	0.001	0.025

SU YILI (2006) YILLIK TOPLAM AKIM 5.73 MİLYON M3 4 MM. 0.1 LT/SN/Km2

10. Burdur Göller Havzasi

D10A023 KARAMANLI BRJ. GİRİŞ

YERİ : **BURDUR-KARAMANLI YOLUNU TAKİBEN KARAMANLI İLÇESİNE VARILIR. KARAMANLI - YEŞİLOVA YOLUNA DÖNÜLÜR. 2 KM SONRA BARAJA VARILIR. BARAJDAN 4.5 KM SONRAKİ DEREBOĞAZI KÖPRÜSÜNÜN SOL TARAFINDADIR. HARİTA PAFTA NO: N23-B1**
29°49'12" Doğu - 37°26'1" Kuzey

YAĞIŞ ALANI : **114,20 km2** **YAKLAŞIK KOT : 1190 m**

GÖZLEM SÜRESİ : **14.09.1974 - 30.09.2006**

ORTALAMA AKIMLAR : **Gözlem süresinde 0.321 m3/sn. (29 Yıllık) 2006 Su yılında 0.134 m3/sn.**

ANLIK EN ÇOK VE EN AZ AKIMLAR:

2006 Su yılında anlık ençok akım	:	**0.520**	**m3/sn**	**14.03.2006**
2006 Su yılında anlık enaz akım	:	**0.000**	**m3/sn**	**01.08.2006**
Gözlem süresinde anlık ençok akım	:	**13.0**	**m3/sn**	**15.04.1976**
Gözlem süresinde anlık enaz akım	:	**0.000**	**m3/sn**	**01.10.1997**

İstasyon için kullanılmış anahtar bulunamadı.

Akımlar 01 Ekim 2005 'den 30 Eylül 2006' a kadar m3/sn olarak

Gün	Ekim	Kasım	Aralık	Ocak	Şubat	Mart	Nisan	Mayıs	Haziran	Temmuz	Ağustos	Eylül
01	0.124	0.124	0.124	0.124	0.124	0.166	0.166	0.330	0.124	0.085	KURU	0.023
02	0.124	0.124	0.124	0.124	0.124	0.124	0.215	0.264	0.124	0.085	KURU	0.023
03	0.085	0.124	0.124	0.124	0.166	0.124	0.264	0.264	0.124	0.085	KURU	0.051
04	0.085	0.124	0.124	0.124	0.166	0.124	0.264	0.215	0.124	0.085	KURU	0.051
05	0.085	0.124	0.124	0.124	0.166	0.124	0.264	0.264	0.124	0.085	KURU	0.085
06	0.085	0.124	0.124	0.124	0.215	0.124	0.264	0.264	0.124	0.085	KURU	0.085
07	0.085	0.124	0.124	0.124	0.215	0.124	0.264	0.264	0.124	0.085	KURU	0.085
08	0.085	0.124	0.124	0.124	0.215	0.124	0.264	0.264	0.124	0.085	KURU	0.085
09	0.124	0.124	0.124	0.124	0.215	0.124	0.264	0.215	0.085	0.085	KURU	0.085
10	0.124	0.124	0.124	0.124	0.215	0.124	0.264	0.215	0.085	0.085	KURU	0.085
11	0.124	0.124	0.124	0.124	0.215	0.124	0.264	0.215	0.085	0.085	KURU	0.085
12	0.124	0.124	0.124	0.124	0.215	0.124	0.264	0.215	0.085	0.085	KURU	0.085
13	0.124	0.124	0.124	0.124	0.215	0.166	0.264	0.215	0.085	0.085	0.023	0.085
14	0.124	0.124	0.124	0.124	0.215	0.520	0.264	0.215	0.085	0.085	0.051	0.085
15	0.124	0.124	0.124	0.124	0.215	0.264	0.330	0.215	0.085	0.085	0.023	0.085
16	0.124	0.124	0.124	0.124	0.215	0.264	0.330	0.215	0.085	0.085	0.023	0.085
17	0.124	0.124	0.124	0.124	0.215	0.215	0.330	0.215	0.085	0.085	KURU	0.085
18	0.124	0.124	0.124	0.124	0.215	0.215	0.330	0.166	0.085	0.085	KURU	0.085
19	0.124	0.124	0.124	0.124	0.215	0.215	0.330	0.166	0.085	0.085	KURU	0.085
20	0.124	0.124	0.124	0.124	0.215	0.215	0.330	0.166	0.085	0.051	KURU	0.085
21	0.124	0.124	0.124	0.124	0.215	0.215	0.330	0.166	0.085	0.051	KURU	0.085
22	0.124	0.124	0.124	0.124	0.215	0.166	0.330	0.166	0.085	0.051	KURU	0.085
23	0.124	0.124	0.124	0.124	0.215	0.166	0.450	0.166	0.085	0.023	KURU	0.085
24	0.124	0.124	0.124	0.124	0.215	0.166	0.450	0.166	0.085	0.023	KURU	0.085
25	0.124	0.124	0.124	0.124	0.215	0.166	0.393	0.166	0.085	0.023	0.023	0.085
26	0.124	0.124	0.124	0.124	0.215	0.166	0.330	0.215	0.085	0.023	0.023	0.085
27	0.124	0.124	0.124	0.124	0.166	0.166	0.330	0.166	0.085	0.023	KURU	0.085
28	0.124	0.124	0.124	0.124	0.166	0.166	0.330	0.124	0.085	0.023	KURU	0.085
29	0.124	0.124	0.124	0.124	-----	0.166	0.330	0.124	0.085	0.023	KURU	0.085
30	0.124	0.124	0.124	0.124	-----	0.166	0.330	0.124	0.085	0.006	KURU	0.085
31	0.124	-----	0.124	0.124	-----	0.166	-----	0.124	-----	0.006	KURU	-----
Maks.	0.124	0.124	0.124	0.124	0.215	0.520	0.450	0.330	0.124	0.085	0.051	0.085
Min.	0.085	0.124	0.124	0.124	0.124	0.124	0.166	0.124	0.085	0.006	KURU	0.023
Ortalama	0.116	0.124	0.124	0.124	0.200	0.177	0.304	0.202	0.095	0.063	0.005	0.079
LT/SN/Km2	1.02	1.09	1.09	1.09	1.75	1.55	2.67	1.77	0.835	0.548	0.047	0.688
AKIM mm.	2.73	2.81	2.91	2.91	4.23	4.15	6.91	4.74	2.17	1.47	0.126	1.78
MİL. M3	0.312	0.321	0.332	0.332	0.483	0.473	0.789	0.542	0.247	0.168	0.014	0.204

SU YILI (2006) YILLIK TOPLAM AKIM 4.22 MİLYON M3 37 MM. 1.2 LT/SN/Km2

10. Burdur Göller Havzasi

D10A027 BÜĞDÜZ D. SULUDERE

YERİ : **BURDUR KARAMANLI YOLUNDAKİ SULUDERE KÖYÜNÜN 800 M. BATISINDA-DIR. HARİTA PAFTA NO M24-D2**
30°10'45" Doğu - 37°39'6" Kuzey

YAĞIŞ ALANI : **214,30 km2** **YAKLAŞIK KOT : 900 m**

GÖZLEM SÜRESİ : **17.03.1978 - 30.09.2006**

ORTALAMA AKIMLAR : **Gözlem süresinde 0.905 m3/sn. (24 Yıllık) 2006 Su yılında 0.105 m3/sn.**

ANLIK EN ÇOK VE EN AZ AKIMLAR:

2006 Su yılında anlık ençok akım	:	**1.38**	**m3/sn**	**14.03.2006**
2006 Su yılında anlık enaz akım	:	**0.000**	**m3/sn**	**08.05.2006**
Gözlem süresinde anlık ençok akım	:	**452.**	**m3/sn**	**21.06.1998**
Gözlem süresinde anlık enaz akım	:	**0.000**	**m3/sn**	**11.07.1996**

7. Anahtar Eğrisi (Seviyeler cm olarak)

Seviye	Akım	Seviye	Akım	Seviye	Akım	Seviye	Akım
1	0.044	15	1.0	70	16.5	120	42.0
3	0.110	20	1.6	80	21.0	130	49.0
5	0.210	40	5.7	90	26.0	140	56.0
7	0.310	50	9.0	100	31.0	150	63.0
9	0.450	60	12.5	110	36.0	200	105.

Akımlar 01 Ekim 2005 'den 30 Eylül 2006' a kadar m3/sn olarak

Gün	Ekim	Kasım	Aralık	Ocak	Şubat	Mart	Nisan	Mayıs	Haziran	Temmuz	Ağustos	Eylül
01	0.072	0.110	0.310	0.110	0.155	0.210	0.044	0.072	KURU	KURU	KURU	KURU
02	0.072	0.110	0.310	0.110	0.155	0.210	0.044	0.072	KURU	KURU	KURU	KURU
03	0.110	0.155	0.310	0.110	0.155	0.210	0.044	0.072	KURU	KURU	KURU	KURU
04	0.110	0.155	0.310	0.110	0.155	0.310	0.044	0.072	KURU	KURU	KURU	KURU
05	0.110	0.155	0.260	0.110	0.155	0.310	0.044	0.044	KURU	KURU	KURU	KURU
06	0.110	0.210	0.260	0.110	0.155	0.155	0.044	0.044	KURU	KURU	KURU	KURU
07	0.110	0.210	0.260	0.110	0.155	0.072	0.044	0.044	KURU	KURU	KURU	KURU
08	0.110	0.210	0.260	0.110	0.155	0.072	0.044	KURU	KURU	KURU	KURU	KURU
09	0.110	0.210	0.260	0.110	0.155	0.072	0.044	KURU	KURU	KURU	KURU	KURU
10	0.110	0.210	0.260	0.110	0.155	0.044	0.072	KURU	KURU	KURU	KURU	KURU
11	0.110	0.210	0.260	0.110	0.155	0.044	0.072	KURU	KURU	KURU	KURU	KURU
12	0.110	0.210	0.210	0.110	0.155	0.044	0.110	KURU	KURU	KURU	KURU	KURU
13	0.110	0.210	0.210	0.110	0.155	0.904	0.110	KURU	KURU	KURU	KURU	KURU
14	0.110	0.210	0.210	0.072	0.155	1.38	0.110	KURU	KURU	KURU	KURU	KURU
15	0.110	0.210	0.155	0.110	0.155	0.808	0.110	KURU	KURU	KURU	KURU	KURU
16	0.110	0.210	0.155	0.110	0.155	0.450	0.110	KURU	KURU	KURU	KURU	KURU
17	0.110	0.210	0.155	0.110	0.155	0.450	0.110	KURU	KURU	KURU	KURU	KURU
18	0.110	0.210	0.155	0.072	0.155	0.520	0.072	KURU	KURU	KURU	KURU	KURU
19	0.110	0.210	0.155	0.110	0.210	0.520	0.072	KURU	KURU	KURU	KURU	KURU
20	0.110	0.260	0.155	0.110	0.210	0.450	0.072	KURU	KURU	KURU	KURU	KURU
21	0.110	0.260	0.155	0.110	0.210	0.450	0.072	KURU	KURU	KURU	KURU	KURU
22	0.110	0.260	0.155	0.110	0.210	0.450	0.072	KURU	KURU	KURU	KURU	KURU
23	0.110	0.260	0.155	0.110	0.210	0.520	0.072	KURU	KURU	KURU	KURU	KURU
24	0.110	0.260	0.155	0.110	0.210	0.616	0.072	KURU	KURU	KURU	KURU	KURU
25	0.110	0.260	0.110	0.110	0.210	0.450	0.072	KURU	KURU	KURU	KURU	KURU
26	0.110	0.310	0.110	0.110	0.210	0.390	0.072	KURU	KURU	KURU	KURU	KURU
27	0.110	0.310	0.110	0.155	0.210	0.260	0.072	KURU	KURU	KURU	KURU	KURU
28	0.110	0.390	0.110	0.155	0.210	0.210	0.072	KURU	KURU	KURU	KURU	KURU
29	0.110	0.390	0.110	0.155	-----	0.210	0.072	KURU	KURU	KURU	KURU	KURU
30	0.110	0.310	0.110	0.155	-----	0.155	0.072	KURU	KURU	KURU	KURU	KURU
31	0.110	-----	0.110	0.155	-----	0.110	-----	KURU	-----	KURU	KURU	-----
Maks.	0.110	0.390	0.310	0.155	0.210	1.38	0.110	0.072	KURU	KURU	KURU	KURU
Min.	0.072	0.110	0.110	0.072	0.155	0.044	0.044	KURU	KURU	KURU	KURU	KURU
Ortalama	0.108	0.230	0.194	0.115	0.175	0.357	0.071	0.014	KURU	KURU	KURU	KURU
LT/SN/Km2	0.502	1.07	0.905	0.536	0.815	1.66	0.332	0.063	0.000	0.000	0.000	0.000
AKIM mm.	1.34	2.78	2.42	1.43	1.97	4.46	0.861	0.169	0.000	0.000	0.000	0.000
MİL. M3	0.288	0.596	0.519	0.307	0.422	0.955	0.185	0.036	0.000	0.000	0.000	0.000

SU YILI (2006) YILLIK TOPLAM AKIM 3.31 MİLYON M3 15 MM. 0.5 LT/SN/Km2

10. Burdur Göller Havzasi

D10A032 DEĞİRMEN DERESİ BAŞMAKCI-YAKA

YERİ : ISPARTA-DİNAR-BAŞMAKÇI YOLUNU TAKİBEN BAŞMAKÇIDAN YAKA KASABASINA VARILIR. KASABANIN GÜNEYİNDE BULUNAN DEĞİRMEN DERESİNİ TAKİBEN 1 KM SONRA DERENİN SOL SAHİLİNE TESİS EDİLMİŞTİR. 30°2'39" Doğu - 37°51'27" Kuzey

YAĞIŞ ALANI : 60,76 km2 **YAKLAŞIK KOT :** 904 m

GÖZLEM SÜRESİ : 19.09.2005 - 30.09.2006

ORTALAMA AKIMLAR : Gözlem süresinde 0.167 m3/sn. (1 Yıllık) 2006 Su yılında 0.167 m3/sn.

ANLIK EN ÇOK VE EN AZ AKIMLAR:

2006 Su yılında anlık ençok akım	:	0.846 m3/sn	12.04.2006
2006 Su yılında anlık enaz akım	:	0.025 m3/sn	01.11.2005
Gözlem süresinde anlık ençok akım	:	0.846 m3/sn	12.04.2006
Gözlem süresinde anlık enaz akım	:	0.025 m3/sn	01.11.2005

1. Anahtar Eğrisi (Seviyeler cm olarak)

Seviye	Akım	Seviye	Akım	Seviye	Akım	Seviye	Akım
10	0.025	25	0.290	40	1.0	100	14.5
13	0.053	28	0.370	43	1.4	130	26.0
16	0.094	31	0.490	46	1.8	140	30.0
19	0.150	34	0.650	49	2.2	150	34.5
22	0.210	37	0.846	70	6.0	160	38.0

Akımlar 01 Ekim 2005 'den 30 Eylül 2006' a kadar m3/sn olarak

Gün	Ekim	Kasım	Aralık	Ocak	Şubat	Mart	Nisan	Mayıs	Haziran	Temmuz	Ağustos	Eylül
01	0.043	0.025	0.130	0.080	0.130	0.170	0.650	0.210	0.094	0.094	0.080	0.080
02	0.043	0.025	0.130	0.080	0.130	0.230	0.650	0.170	0.094	0.094	0.080	0.080
03	0.043	0.025	0.130	0.080	0.130	0.230	0.650	0.170	0.094	0.094	0.080	0.080
04	0.043	0.043	0.130	0.080	0.130	0.230	0.650	0.190	0.094	0.094	0.080	0.080
05	0.043	0.043	0.130	0.080	0.130	0.260	0.650	0.210	0.094	0.094	0.080	0.080
06	0.053	0.043	0.130	0.080	0.130	0.260	0.650	0.230	0.094	0.094	0.080	0.080
07	0.053	0.043	0.110	0.080	0.130	0.290	0.710	0.210	0.094	0.094	0.080	0.080
08	0.053	0.065	0.110	0.080	0.130	0.290	0.710	0.190	0.094	0.094	0.080	0.080
09	0.053	0.065	0.110	0.065	0.170	0.490	0.710	0.190	0.094	0.094	0.080	0.080
10	0.053	0.094	0.110	0.065	0.170	0.600	0.778	0.190	0.094	0.094	0.080	0.080
11	0.053	0.094	0.110	0.065	0.170	0.710	0.778	0.190	0.094	0.094	0.080	0.080
12	0.053	0.094	0.094	0.065	0.170	0.530	0.846	0.190	0.094	0.094	0.080	0.080
13	0.053	0.130	0.094	0.065	0.170	0.490	0.778	0.190	0.094	0.094	0.080	0.080
14	0.065	0.130	0.094	0.065	0.170	0.490	0.650	0.190	0.094	0.094	0.080	0.080
15	0.065	0.130	0.094	0.065	0.170	0.400	0.650	0.190	0.094	0.094	0.080	0.080
16	0.065	0.130	0.094	0.065	0.170	0.370	0.778	0.150	0.094	0.080	0.080	0.080
17	0.065	0.150	0.094	0.065	0.170	0.370	0.710	0.190	0.094	0.080	0.080	0.080
18	0.065	0.150	0.094	0.065	0.170	0.370	0.600	0.130	0.094	0.080	0.080	0.080
19	0.065	0.150	0.094	0.065	0.170	0.400	0.530	0.130	0.094	0.080	0.080	0.080
20	0.065	0.170	0.094	0.065	0.170	0.440	0.490	0.130	0.094	0.080	0.080	0.080
21	0.080	0.170	0.080	0.080	0.170	0.490	0.440	0.130	0.094	0.080	0.080	0.080
22	0.080	0.170	0.080	0.080	0.170	0.490	0.400	0.110	0.094	0.080	0.080	0.065
23	0.080	0.150	0.080	0.080	0.170	0.490	0.400	0.110	0.094	0.080	0.080	0.065
24	0.080	0.150	0.080	0.080	0.170	0.530	0.400	0.110	0.094	0.080	0.080	0.065
25	0.080	0.150	0.080	0.094	0.170	0.600	0.370	0.110	0.094	0.080	0.080	0.065
26	0.065	0.130	0.080	0.094	0.170	0.600	0.340	0.110	0.094	0.080	0.080	0.065
27	0.065	0.130	0.080	0.094	0.170	0.530	0.320	0.110	0.094	0.080	0.080	0.065
28	0.053	0.130	0.080	0.094	0.170	0.600	0.290	0.110	0.094	0.080	0.080	0.065
29	0.053	0.130	0.080	0.094	-----	0.600	0.290	0.110	0.094	0.080	0.080	0.065
30	0.043	0.130	0.080	0.094	-----	0.650	0.230	0.094	0.094	0.080	0.080	0.065
31	0.034	-----	0.080	0.094	-----	0.650	-----	0.094	-----	0.080	0.080	-----
Maks.	0.080	0.170	0.130	0.094	0.170	0.710	0.846	0.230	0.094	0.094	0.080	0.080
Min.	0.034	0.025	0.080	0.065	0.130	0.170	0.230	0.094	0.094	0.080	0.080	0.065
Ortalama	0.058	0.108	0.099	0.077	0.159	0.447	0.570	0.156	0.094	0.087	0.080	0.076
LT/SN/Km2	0.959	1.78	1.62	1.27	2.61	7.35	9.38	2.57	1.55	1.43	1.32	1.24
AKIM mm.	2.57	4.61	4.35	3.41	6.31	19.7	24.3	6.88	4.01	3.83	3.53	3.22
MİL. M3	0.156	0.280	0.264	0.207	0.384	1.20	1.48	0.418	0.244	0.232	0.214	0.196

SU YILI (2006) YILLIK TOPLAM AKIM 5.28 MİLYON M3 87 MM. 2.7 LT/SN/Km2

10. Burdur Göller Havzasi

D10A033 BAYNAZ DERESİ ÇAYLI

YERİ : **BURDUR-TEFENNİ YOLUNU TAKİBEN SOLA DÖNÜLEREK ÇAYLI KÖYÜNE VARILIR. ISTASYON KÖYÜN ÇIKIŞINDAKİ KÖPRÜYE TESİS EDİLMİŞTİR.**
29°48'37" Doğu - 37°12'25" Kuzey

YAĞIŞ ALANI : **39,29 km2** **YAKLAŞIK KOT : 1316 m**

GÖZLEM SÜRESİ : **09.11.2005 - 30.09.2006**

ORTALAMA AKIMLAR : **Gözlem süresinde -- m3/sn. (- Yıllık) 2006 Su yılında -- m3/sn.**

ANLIK EN ÇOK VE EN AZ AKIMLAR:

2006 Su yılında anlık ençok akım : -- m3/sn

2006 Su yılında anlık enaz akım : -- m3/sn

Gözlem süresinde anlık ençok akım : -- m3/sn

Gözlem süresinde anlık enaz akım : -- m3/sn

1. Anahtar Eğrisi (Seviyeler cm olarak)

Seviye	Akım	Seviye	Akım	Seviye	Akım	Seviye	Akım
3	0.003	13	0.080	23	0.460	33	1.8
5	0.008	15	0.120	25	0.600	35	2.2
7	0.017	17	0.187	27	0.820	37	3.0
9	0.029	19	0.253	29	1.0	39	3.8
11	0.050	21	0.320	31	1.4	40	4.2

Akımlar 01 Ekim 2005 'den 30 Eylül 2006' a kadar m3/sn olarak

Gün	Ekim	Kasım	Aralık	Ocak	Şubat	Mart	Nisan	Mayıs	Haziran	Temmuz	Ağustos	Eylül
01	-----	-----	0.038	0.080	0.065	0.100	0.600	0.220	0.050	0.012	0.012	0.022
02	-----	-----	0.065	0.065	0.065	0.220	0.460	0.220	0.050	0.012	0.012	0.022
03	-----	-----	0.253	0.065	0.065	0.460	0.460	0.220	0.050	0.012	0.012	0.022
04	-----	-----	0.253	0.065	0.065	0.460	0.390	0.253	0.050	0.012	0.012	0.022
05	-----	-----	0.253	0.065	0.065	0.460	0.390	0.287	0.050	0.012	0.012	0.017
06	-----	-----	0.253	0.065	0.065	0.460	0.390	0.320	0.050	0.017	0.012	0.017
07	-----	-----	0.253	0.065	0.065	0.460	0.460	0.320	0.050	0.017	0.012	0.017
08	-----	-----	0.253	0.065	0.100	0.460	0.460	0.320	0.050	0.017	0.012	0.017
09	-----	0.038	0.253	0.065	0.153	0.460	0.460	0.390	0.050	0.017	0.012	0.017
10	-----	0.038	0.253	0.065	0.153	0.460	0.460	0.390	0.065	0.017	0.012	0.017
11	-----	0.038	0.253	0.065	0.220	0.460	0.460	0.390	0.100	0.022	0.012	0.017
12	-----	0.038	0.220	0.065	0.287	0.460	0.460	0.287	0.050	0.022	0.012	0.017
13	-----	0.038	0.220	0.065	0.320	0.460	0.460	0.287	0.050	0.022	0.012	0.017
14	-----	0.038	0.187	0.065	0.253	0.460	0.460	0.220	0.080	0.022	0.012	0.017
15	-----	0.038	0.187	0.065	0.220	0.530	0.460	0.220	0.050	0.022	0.012	0.017
16	-----	0.029	0.187	0.065	0.153	0.530	0.460	0.220	0.050	0.022	0.012	0.017
17	-----	0.029	0.153	0.065	0.120	0.600	0.460	0.120	0.050	0.022	0.012	0.017
18	-----	0.220	0.120	0.065	0.100	0.600	0.460	0.120	0.038	0.022	0.022	0.017
19	-----	0.187	0.120	0.065	0.120	0.710	0.390	0.120	0.022	0.022	0.022	0.017
20	-----	0.287	0.120	0.065	0.120	0.710	0.390	0.100	0.012	0.022	0.022	0.017
21	-----	0.080	0.120	0.065	0.153	0.820	0.320	0.100	0.012	0.022	0.022	0.017
22	-----	0.050	0.120	0.065	0.100	0.820	0.320	0.080	0.012	0.022	0.022	0.017
23	-----	0.065	0.100	0.065	0.100	0.930	0.287	0.065	0.012	0.022	0.022	0.017
24	-----	0.065	0.100	0.065	0.100	0.710	0.287	0.050	0.012	0.017	0.022	0.017
25	-----	0.080	0.100	0.065	0.100	0.600	0.253	0.050	0.012	0.017	0.022	0.017
26	-----	0.065	0.100	0.065	0.100	0.600	0.253	0.050	0.012	0.017	0.022	0.029
27	-----	0.050	0.065	0.065	0.080	0.600	0.253	0.050	0.012	0.012	0.022	0.080
28	-----	0.050	0.065	0.065	0.080	0.820	0.253	0.050	0.012	0.012	0.022	0.080
29	-----	0.038	0.065	0.065	-----	0.600	0.220	0.050	0.012	0.012	0.022	0.038
30	-----	0.038	0.080	0.065	-----	0.600	0.220	0.050	0.012	0.012	0.022	0.029
31	-----	-----	0.080	0.065	-----	0.600	-----	0.050	-----	0.012	0.022	-----
Maks.	--	--	0.253	0.080	0.320	0.930	0.600	0.390	0.100	0.022	0.022	0.080
Min.	--	--	0.038	0.065	0.065	0.100	0.220	0.050	0.012	0.012	0.012	0.017
Ortalama	--	--	0.158	0.065	0.128	0.555	0.389	0.183	0.038	0.017	0.017	0.023
LT/SN/Km2	--	--	4.01	1.67	3.26	14.1	9.89	4.65	0.965	0.445	0.420	0.595
AKIM mm.	--	--	10.8	4.46	7.89	37.9	25.6	12.5	2.50	1.19	1.13	1.54
MİL. M3	--	--	0.422	0.175	0.310	1.49	1.01	0.490	0.098	0.047	0.044	0.061

SU YILI (2006)

11

AKARÇAY HAVZASI

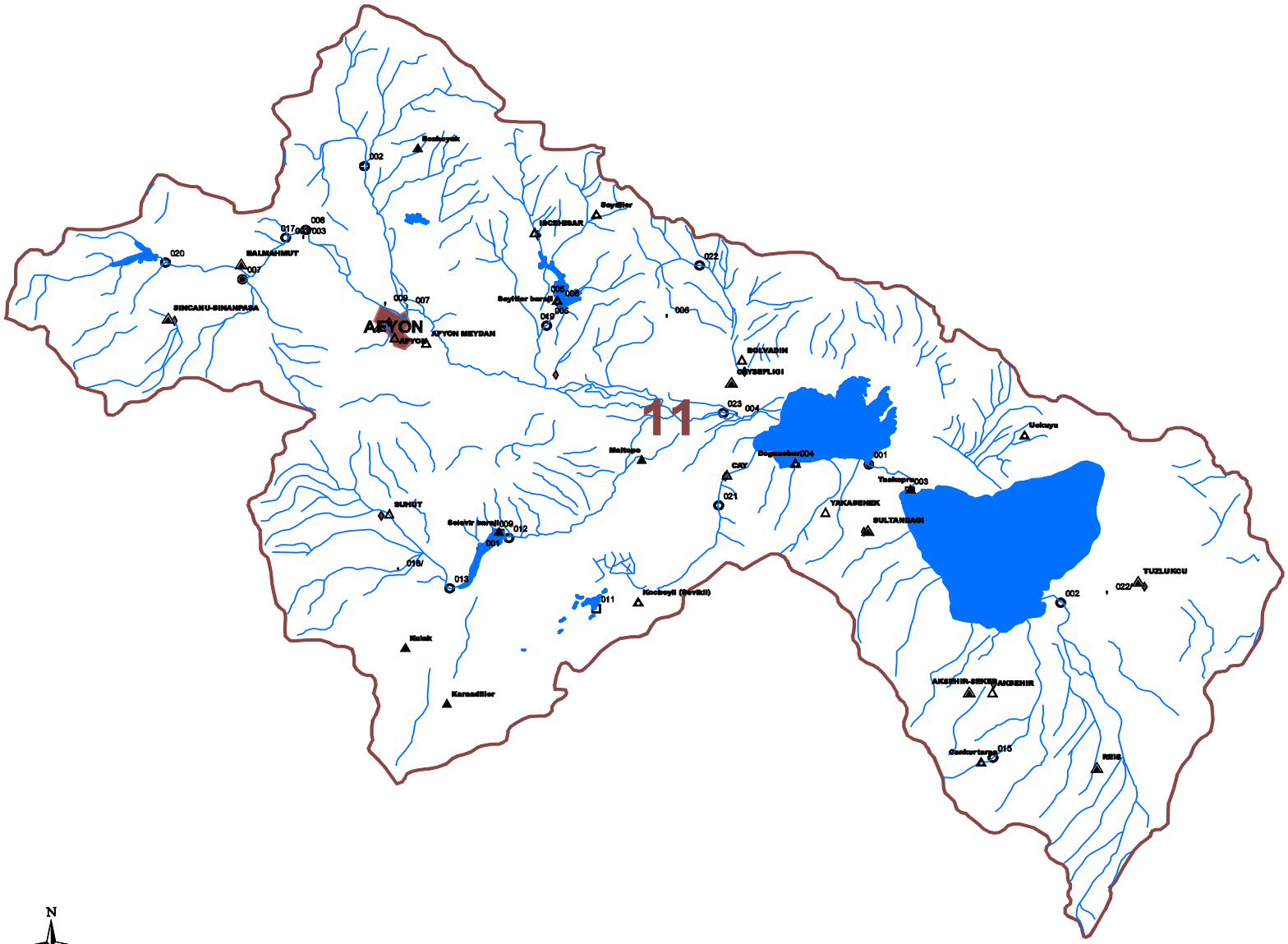

11 AKARCAY HAVZASI

- DSI-AGI(Açik)
- DSI-AGI(Kapali)
- DSI-GGI(Açik)
- EIE-AGI(Açik)
- EIE-AGI(Kapali)
- DSI-MGI(Açik)
- DSI-MGI(Kapali)
- DMI-MGI(Açik)
- DMI-MGI(Kapali)

N

1:500.000

11. Akarçay Havzasi

D11A002 ADIYAN S. ORTAKÖY

YERİ : **AKŞEHİR- YUNAK YOLUNUN 16 KM SİNDEKİ KÖPRÜDEDİR.**
31°30'58" Doğu - 38°26'50" Kuzey

YAĞIŞ ALANI : **631,90 km2** **YAKLAŞIK KOT : 965 m**

GÖZLEM SÜRESİ : **18.05.1959 - 30.09.2006**

ORTALAMA AKIMLAR : **Gözlem süresinde 1.895 m3/sn. (47 Yıllık) 2006 Su yılında 0.529 m3/sn.**

ANLIK EN ÇOK VE EN AZ AKIMLAR:

2006 Su yılında anlık ençok akım	**:**	**6.60**	**m3/sn**	**25.04.2006**
2006 Su yılında anlık enaz akım	**:**	**0.000**	**m3/sn**	**01.10.2005**
Gözlem süresinde anlık ençok akım	**:**	**70.0**	**m3/sn**	**14.12.1976**
Gözlem süresinde anlık enaz akım	**:**	**0.000**	**m3/sn**	**12.07.1961**

4. Anahtar Eğrisi (Seviyeler cm olarak)

Seviye	Akım	Seviye	Akım	Seviye	Akım	Seviye	Akım
1	0.000	26	0.210	61	1.6	151	9.0
6	0.001	31	0.340	71	2.1	201	16.0
11	0.008	36	0.500	81	2.7	251	25.0
16	0.037	41	0.680	91	3.4	301	35.0
21	0.100	51	1.0	101	4.0		

Akımlar 01 Ekim 2005 'den 30 Eylül 2006' a kadar m3/sn olarak

Gün	Ekim	Kasım	Aralık	Ocak	Şubat	Mart	Nisan	Mayıs	Haziran	Temmuz	Ağustos	Eylül
01	KURU	KURU	KURU	KURU	KURU	1.30	3.65	1.80	0.006	KURU	KURU	KURU
02	KURU	KURU	KURU	KURU	KURU	1.30	3.40	2.15	0.006	KURU	KURU	KURU
03	KURU	KURU	KURU	KURU	KURU	1.45	3.10	2.20	0.002	KURU	KURU	KURU
04	KURU	KURU	KURU	KURU	KURU	2.00	2.95	2.30	KURU	KURU	KURU	KURU
05	KURU	KURU	KURU	KURU	KURU	1.70	2.60	2.00	KURU	KURU	KURU	KURU
06	KURU	KURU	KURU	KURU	KURU	1.50	2.25	2.50	KURU	KURU	KURU	KURU
07	KURU	KURU	KURU	KURU	KURU	1.45	2.15	2.95	KURU	KURU	KURU	KURU
08	KURU	KURU	KURU	KURU	0.003	1.40	2.25	2.55	KURU	KURU	KURU	KURU
09	KURU	KURU	KURU	KURU	0.120	1.40	2.20	2.50	KURU	KURU	KURU	KURU
10	KURU	KURU	KURU	KURU	0.400	1.15	2.25	2.15	KURU	KURU	KURU	KURU
11	KURU	KURU	KURU	KURU	1.10	1.05	2.10	1.93	KURU	KURU	KURU	KURU
12	KURU	KURU	KURU	KURU	0.600	1.02	1.85	1.70	KURU	KURU	KURU	KURU
13	KURU	KURU	KURU	KURU	2.00	0.900	1.85	1.55	KURU	KURU	KURU	KURU
14	KURU	KURU	KURU	KURU	1.50	0.940	1.75	1.45	KURU	KURU	KURU	KURU
15	KURU	KURU	KURU	KURU	1.25	1.60	1.60	1.10	KURU	KURU	KURU	KURU
16	KURU	KURU	KURU	KURU	0.940	1.45	1.75	0.980	KURU	KURU	KURU	KURU
17	KURU	KURU	KURU	KURU	0.760	1.40	1.65	0.900	KURU	KURU	KURU	KURU
18	KURU	KURU	KURU	KURU	0.830	1.55	1.40	1.05	KURU	KURU	KURU	KURU
19	KURU	KURU	KURU	KURU	0.940	2.05	1.20	1.10	KURU	KURU	KURU	KURU
20	KURU	KURU	KURU	KURU	0.865	2.00	0.900	0.865	KURU	KURU	KURU	KURU
21	KURU	KURU	KURU	KURU	0.980	1.80	0.680	0.540	KURU	KURU	KURU	KURU
22	KURU	KURU	KURU	KURU	1.02	2.10	0.570	0.400	KURU	KURU	KURU	KURU
23	KURU	KURU	KURU	KURU	1.05	3.00	0.865	0.280	KURU	KURU	KURU	KURU
24	KURU	KURU	KURU	KURU	1.10	4.10	2.80	0.120	KURU	KURU	KURU	KURU
25	KURU	KURU	KURU	KURU	1.25	4.76	6.60	0.088	KURU	KURU	KURU	KURU
26	KURU	KURU	KURU	KURU	1.35	4.60	4.36	0.046	KURU	KURU	KURU	KURU
27	KURU	KURU	KURU	KURU	1.50	3.95	3.20	0.020	KURU	KURU	KURU	KURU
28	KURU	KURU	KURU	KURU	1.45	3.50	2.30	0.015	KURU	KURU	KURU	KURU
29	KURU	KURU	KURU	KURU	-----	3.25	2.20	0.015	KURU	KURU	KURU	KURU
30	KURU	KURU	KURU	KURU	-----	3.20	2.05	0.008	KURU	KURU	KURU	KURU
31	KURU	-----	KURU	KURU	-----	3.50	-----	0.006	-----	KURU	KURU	-----
Maks.	KURU	KURU	KURU	KURU	2.00	4.76	6.60	2.95	0.006	KURU	KURU	KURU
Min.	KURU	KURU	KURU	KURU	KURU	0.900	0.570	0.006	KURU	KURU	KURU	KURU
Ortalama	KURU	KURU	KURU	KURU	0.750	2.14	2.28	1.20	0.000	KURU	KURU	KURU
LT/SN/Km2	0.000	0.000	0.000	0.000	1.19	3.39	3.61	1.90	0.001	0.000	0.000	0.000
AKIM mm.	0.000	0.000	0.000	0.000	2.87	9.07	9.36	5.09	0.002	0.000	0.000	0.000
MİL. M3	0.000	0.000	0.000	0.000	1.82	5.73	5.92	3.22	0.001	0.000	0.000	0.000

SU YILI (2006) YILLIK TOPLAM AKIM 16.69 MİLYON M3 26 MM. 0.8 LT/SN/Km2

11. Akarçay Havzasi

D11A013 KALİ Ç. SELEVİR BRJ. GİRİŞ

YERİ : ŞUHUT-KARAADİLLI YOLUNDA SOLDAKI ÇOBANKAYA KÖYÜNDEN GEÇILIR.SAĞ TARAFA KARAHALLI KÖYÜ YÖNÜNE GIDERKEN AGI'NA VARILIR AGI SAĞ SAHILDE OLUP LIMNIGRAFLIDIR. 30°38'47" Doğu - 38°26'56" Kuzey

YAĞIŞ ALANI : 690,00 km2 **YAKLAŞIK KOT** : 1110 m

GÖZLEM SÜRESİ : 25.09.1965 - 30.09.2006

ORTALAMA AKIMLAR : Gözlem süresinde 1.577 m3/sn. (40 Yıllık) 2006 Su yılında 0.800 m3/sn.

ANLIK EN ÇOK VE EN AZ AKIMLAR:

2006 Su yılında anlık ençok akım	:	9.10	m3/sn	15.03.2006
2006 Su yılında anlık enaz akım	:	0.000	m3/sn	01.10.2005
Gözlem süresinde anlık ençok akım	:	270.	m3/sn	11.03.1968
Gözlem süresinde anlık enaz akım	:	0.000	m3/sn	22.07.1975

1. Anahtar Eğrisi (Seviyeler cm olarak)

Seviye	Akım	Seviye	Akım	Seviye	Akım	Seviye	Akım
1	0.010	21	2.4	42	7.5	82	21.0
5	0.170	25	3.2	50	9.7	92	25.0
9	0.550	29	4.1	58	12.0	110	34.0
13	1.0	33	5.1	66	15.0	150	53.0
17	1.7	37	6.1	74	18.0	240	95.0

Akımlar 01 Ekim 2005 'den 30 Eylül 2006' a kadar m3/sn olarak

Gün	Ekim	Kasım	Aralık	Ocak	Şubat	Mart	Nisan	Mayıs	Haziran	Temmuz	Ağustos	Eylül
01	KURU	KURU	0.250	0.010	0.010	2.60	4.90	1.85	0.940	KURU	KURU	KURU
02	KURU	KURU	0.170	0.010	0.010	2.60	3.60	1.50	0.800	KURU	KURU	KURU
03	KURU	KURU	0.170	0.010	0.010	5.40	3.40	1.20	0.800	KURU	KURU	KURU
04	KURU	KURU	0.170	0.010	0.010	5.10	3.90	0.940	0.800	KURU	KURU	KURU
05	KURU	KURU	0.170	0.010	0.010	3.00	2.40	0.940	0.800	KURU	KURU	KURU
06	KURU	KURU	0.170	0.010	0.010	2.40	2.20	0.940	KURU	KURU	KURU	KURU
07	KURU	KURU	0.170	0.010	0.010	2.00	2.40	0.940	KURU	KURU	KURU	KURU
08	KURU	KURU	0.170	0.010	0.010	1.85	2.60	0.940	KURU	KURU	KURU	KURU
09	KURU	KURU	0.170	0.010	0.010	2.40	2.80	0.800	KURU	KURU	KURU	KURU
10	KURU	KURU	0.170	0.010	0.010	1.85	2.40	0.800	KURU	KURU	KURU	KURU
11	KURU	KURU	0.170	0.010	0.010	1.70	2.20	0.800	KURU	KURU	KURU	KURU
12	KURU	KURU	0.170	0.010	0.340	1.70	2.20	0.800	KURU	KURU	KURU	KURU
13	KURU	KURU	0.110	0.010	1.50	3.40	3.00	0.800	KURU	KURU	KURU	KURU
14	KURU	KURU	0.010	0.010	0.340	6.60	3.90	0.800	KURU	KURU	KURU	KURU
15	KURU	KURU	0.030	0.010	0.670	9.10	6.40	0.800	KURU	KURU	KURU	KURU
16	KURU	KURU	0.030	0.010	0.800	7.20	4.40	0.800	KURU	KURU	KURU	KURU
17	KURU	KURU	0.060	0.010	0.800	6.10	3.40	0.800	KURU	KURU	KURU	KURU
18	KURU	KURU	0.060	0.010	0.800	4.40	2.80	0.670	KURU	KURU	KURU	KURU
19	KURU	KURU	0.060	0.010	1.70	4.60	2.20	0.670	KURU	KURU	KURU	KURU
20	KURU	KURU	0.030	0.010	2.20	4.10	2.00	0.670	KURU	KURU	KURU	KURU
21	KURU	KURU	0.030	0.010	3.00	4.10	1.85	0.670	KURU	KURU	KURU	KURU
22	KURU	KURU	0.030	0.010	3.00	4.90	1.85	0.670	KURU	KURU	KURU	KURU
23	KURU	KURU	0.030	0.010	2.80	5.90	2.80	0.670	KURU	KURU	KURU	KURU
24	KURU	KURU	0.030	0.010	2.60	7.75	5.60	1.05	KURU	KURU	KURU	KURU
25	KURU	KURU	0.030	0.010	2.80	6.40	2.80	0.940	KURU	KURU	KURU	KURU
26	KURU	KURU	0.030	0.010	3.20	5.60	2.60	0.940	KURU	KURU	KURU	KURU
27	KURU	KURU	0.030	0.010	3.40	4.90	2.20	1.05	KURU	KURU	KURU	KURU
28	KURU	KURU	0.030	0.010	2.40	4.10	2.20	0.940	KURU	KURU	KURU	KURU
29	KURU	KURU	0.030	0.010	-----	3.40	2.00	0.940	KURU	KURU	KURU	KURU
30	KURU	0.250	0.030	0.010	-----	4.10	2.00	0.940	KURU	KURU	KURU	KURU
31	KURU	-----	0.030	0.010	-----	5.60	-----	0.940	-----	KURU	KURU	-----
Maks.	KURU	0.250	0.250	0.010	3.40	9.10	6.40	1.85	0.940	KURU	KURU	KURU
Min.	KURU	KURU	0.010	0.010	0.010	1.70	1.85	0.670	KURU	KURU	KURU	KURU
Ortalama	KURU	0.008	0.092	0.010	1.16	4.35	2.97	0.910	0.138	KURU	KURU	KURU
LT/SN/Km2	0.000	0.012	0.133	0.014	1.68	6.30	4.30	1.32	0.200	0.000	0.000	0.000
AKIM mm.	0.000	0.031	0.356	0.039	4.06	16.9	11.1	3.53	0.518	0.000	0.000	0.000
MİL. M3	0.000	0.022	0.245	0.027	2.80	11.7	7.69	2.44	0.358	0.000	0.000	0.000

SU YILI (2006) YILLIK TOPLAM AKIM 25.28 MİLYON M3 37 MM. 1.2 LT/SN/Km2

11. Akarçay Havzasi

D11A015 ENGİLLİ D. CANKURTARAN

YERİ : **AKŞEHİR-GELENDOST YOLUNUN 14 KM SİNDEKİ CANKURTARAN MEVKİİNDEDİR. 31°25'12" Doğu - 38°16'28" Kuzey**

YAĞIŞ ALANI : **46,83 km2** **YAKLAŞIK KOT : 1502 m**

GÖZLEM SÜRESİ : **25.09.1965 - 30.09.2006**

ORTALAMA AKIMLAR : **Gözlem süresinde 0.414 m3/sn. (36 Yıllık) 2006 Su yılında 0.212 m3/sn.**

ANLIK EN ÇOK VE EN AZ AKIMLAR:

2006 Su yılında anlık ençok akım	:	**2.70**	**m3/sn**	**25.03.2006**
2006 Su yılında anlık enaz akım	:	**0.000**	**m3/sn**	**24.01.2006**
Gözlem süresinde anlık ençok akım	:	**16.5**	**m3/sn**	**30.08.1979**
Gözlem süresinde anlık enaz akım	:	**0.000**	**m3/sn**	**28.08.1971**

9. Anahtar Eğrisi (Seviyeler cm olarak)

Akımlar 01 Ekim 2005 'den 30 Eylül 2006' a kadar m3/sn olarak

Gün	Ekim	Kasım	Aralık	Ocak	Şubat	Mart	Nisan	Mayıs	Haziran	Temmuz	Ağustos	Eylül
01	0.003	0.009	0.056	0.056	KURU	0.800	1.90	0.380	0.034	0.019	KURU	KURU
02	0.003	0.009	0.056	0.056	KURU	0.900	1.70	0.450	0.034	0.009	KURU	KURU
03	0.009	0.009	0.056	0.056	KURU	1.35	1.50	0.380	0.034	0.009	KURU	KURU
04	0.003	0.009	0.056	0.056	KURU	1.50	1.25	0.380	0.019	0.019	KURU	KURU
05	0.003	0.019	0.056	0.056	KURU	1.25	1.15	0.380	0.019	0.009	KURU	KURU
06	0.003	0.019	0.034	0.056	KURU	1.00	1.00	0.380	0.019	0.003	KURU	KURU
07	0.003	0.019	0.034	0.056	0.003	1.00	1.15	0.310	0.019	0.003	KURU	KURU
08	0.003	0.019	0.056	0.056	0.019	1.00	1.15	0.310	0.019	0.003	KURU	KURU
09	0.003	0.019	0.056	0.056	0.034	0.900	0.900	0.310	0.034	0.003	KURU	KURU
10	0.003	0.034	0.056	0.056	0.056	0.720	0.800	0.255	0.034	0.003	KURU	KURU
11	0.003	0.034	0.056	0.056	0.084	0.620	0.900	0.255	0.056	0.003	KURU	KURU
12	0.003	0.034	0.056	0.056	0.084	0.450	0.900	0.200	0.056	0.003	KURU	KURU
13	0.003	0.034	0.056	0.056	0.084	0.540	0.800	0.200	0.034	0.003	KURU	KURU
14	0.003	0.019	0.056	0.056	0.084	0.540	0.800	0.200	0.115	0.003	KURU	KURU
15	0.003	0.019	0.056	0.056	0.084	0.450	0.720	0.200	0.056	0.003	KURU	KURU
16	0.009	0.019	0.056	0.056	0.084	0.450	0.720	0.155	0.034	0.003	KURU	KURU
17	0.009	0.034	0.056	0.034	0.056	0.450	0.540	0.155	0.019	0.003	KURU	KURU
18	0.003	0.056	0.084	0.034	0.056	0.450	0.380	0.155	0.019	0.003	KURU	KURU
19	0.003	0.115	0.084	0.009	0.084	0.540	0.380	0.155	0.019	0.003	KURU	KURU
20	0.003	0.155	0.084	0.009	0.115	0.540	0.380	0.115	0.019	0.003	KURU	KURU
21	0.003	0.115	0.084	0.009	0.155	0.720	0.310	0.115	0.009	0.003	KURU	KURU
22	0.009	0.115	0.084	0.003	0.255	1.15	0.310	0.115	0.009	0.003	KURU	KURU
23	0.009	0.056	0.084	KURU	0.380	1.80	0.310	0.084	0.009	0.003	KURU	0.003
24	0.009	0.056	0.084	KURU	0.620	2.20	1.35	0.084	0.009	KURU	KURU	0.003
25	0.009	0.056	0.084	KURU	0.800	2.70	0.800	0.056	0.019	KURU	KURU	0.003
26	0.009	0.056	0.084	KURU	1.00	2.40	0.620	0.056	0.009	KURU	KURU	0.003
27	0.009	0.056	0.084	KURU	1.00	1.90	0.450	0.084	0.009	KURU	KURU	0.003
28	0.009	0.056	0.056	KURU	0.800	1.70	0.380	0.056	0.009	KURU	KURU	0.003
29	0.009	0.056	0.056	KURU	-----	1.70	0.380	0.056	0.009	KURU	KURU	0.003
30	0.009	0.056	0.056	KURU	-----	1.80	0.380	0.056	0.019	KURU	KURU	0.003
31	0.009	-----	0.056	KURU	-----	2.10	-----	0.034	-----	KURU	KURU	-----
Maks.	0.009	0.200	0.084	0.056	1.00	2.70	1.90	0.450	0.115	0.019	KURU	0.003
Min.	0.003	0.009	0.034	KURU	KURU	0.450	0.310	0.034	0.009	KURU	KURU	KURU
Ortalama	0.006	0.045	0.064	0.032	0.212	1.15	0.810	0.197	0.027	0.004	KURU	0.001
LT/SN/Km2	0.118	0.969	1.36	0.685	4.53	24.5	17.3	4.22	0.571	0.082	0.000	0.017
AKIM mm.	0.315	2.51	3.64	1.83	11.0	65.7	44.9	11.3	1.48	0.220	0.000	0.044
MİL. M3	0.015	0.118	0.170	0.086	0.513	3.08	2.10	0.529	0.069	0.010	0.000	0.002

SU YILI (2006) YILLIK TOPLAM AKIM 6.69 MİLYON M3 143 MM. 4.5 LT/SN/Km2

11. Akarçay Havzasi

D11A017 ARAPLI D. KÖPRÜLÜ

YERİ : **AFYON-KÜTAHYA KARAYOLUN DAKİ ÖMERLI KAPLICALARINDAN SOLA DÖNÜLEREK KÖPRÜLÜ KÖYÜNE VARILIR.KÖYDEN 500 M.MEMBADAKI KÖPRÜ DE LIMNIGRAFLIDIR.**
30°23'41" Doğu - 38°50'55" Kuzey

YAĞIŞ ALANI : **743,10 km2** **YAKLAŞIK KOT : 1045 m**

GÖZLEM SÜRESİ : **01.04.1970 - 30.09.2006**

ORTALAMA AKIMLAR : **Gözlem süresinde 2.059 m3/sn. (36 Yıllık) 2006 Su yılında 1.216 m3/sn.**

ANLIK EN ÇOK VE EN AZ AKIMLAR:

2006 Su yılında anlık ençok akım	**:**	**11.0**	**m3/sn**	**14.03.2006**
2006 Su yılında anlık enaz akım	**:**	**0.000**	**m3/sn**	**30.07.2006**
Gözlem süresinde anlık ençok akım	**:**	**41.4**	**m3/sn**	**18.12.2001**
Gözlem süresinde anlık enaz akım	**:**	**0.000**	**m3/sn**	**04.10.1987**

6. Anahtar Eğrisi (Seviyeler cm olarak)

Akımlar 01 Ekim 2005 'den 30 Eylül 2006' a kadar m3/sn olarak

Gün	Ekim	Kasım	Aralık	Ocak	Şubat	Mart	Nisan	Mayıs	Haziran	Temmuz	Ağustos	Eylül
01	0.034	0.150	0.420	0.480	0.656	7.64	4.40	1.70	0.656	0.330	KURU	KURU
02	0.034	0.180	0.420	0.480	0.656	7.64	3.80	1.52	0.608	0.330	KURU	KURU
03	0.070	0.230	0.420	0.420	0.656	7.28	3.50	1.52	0.608	0.270	KURU	KURU
04	0.070	0.270	0.420	0.420	0.656	6.92	3.20	1.36	0.560	0.270	KURU	KURU
05	0.070	0.480	0.420	0.420	0.656	6.92	3.00	1.36	0.560	0.270	KURU	KURU
06	0.070	0.420	0.420	0.560	0.656	6.74	2.80	1.20	0.560	0.230	KURU	KURU
07	0.034	0.380	0.420	0.608	0.656	6.74	2.73	1.20	0.560	0.230	KURU	KURU
08	0.050	0.380	0.420	0.608	0.560	6.92	2.66	1.20	0.560	0.230	KURU	KURU
09	0.050	0.380	0.420	0.560	0.380	6.38	2.73	1.20	0.540	0.180	KURU	KURU
10	0.034	0.380	0.420	0.540	0.656	5.24	2.52	1.20	0.540	0.180	KURU	KURU
11	0.034	0.380	0.420	0.540	2.45	4.64	2.38	1.20	0.540	0.150	KURU	KURU
12	0.050	0.380	0.420	0.480	5.12	5.12	2.31	1.04	0.540	0.150	KURU	KURU
13	0.070	0.380	0.420	0.480	3.00	6.74	2.24	1.04	0.540	0.120	KURU	KURU
14	0.070	0.380	0.420	0.480	2.17	11.0	2.17	0.800	0.480	0.120	KURU	KURU
15	0.070	0.380	0.420	0.480	1.70	9.40	3.80	0.800	0.480	0.070	KURU	KURU
16	0.090	0.380	0.480	0.480	1.70	5.96	2.90	0.800	0.480	0.034	KURU	KURU
17	0.150	0.380	0.420	0.420	1.44	5.24	2.45	0.800	0.480	0.011	KURU	KURU
18	0.150	0.380	0.420	0.480	1.60	4.52	2.24	0.800	0.480	0.011	KURU	KURU
19	0.120	0.380	0.420	0.420	5.00	4.40	2.10	0.800	0.420	0.011	KURU	KURU
20	0.150	0.380	0.560	1.12	4.64	3.70	2.66	0.800	0.420	0.011	KURU	KURU
21	0.150	0.420	0.480	1.12	5.72	3.60	1.80	0.800	0.420	0.011	KURU	KURU
22	0.150	0.608	0.656	0.704	5.36	4.04	1.90	0.752	0.420	0.011	KURU	KURU
23	0.150	0.560	0.560	0.656	5.36	5.12	2.38	0.752	0.420	0.011	KURU	KURU
24	0.150	0.480	0.480	0.656	5.36	6.56	2.59	0.752	0.380	0.011	KURU	KURU
25	0.150	0.480	0.420	0.800	9.60	5.84	2.24	0.752	0.380	0.006	KURU	KURU
26	0.150	0.420	0.420	0.656	9.00	5.12	2.10	0.656	0.380	0.006	KURU	KURU
27	0.150	0.608	0.330	0.608	8.80	4.64	2.10	0.656	0.380	0.006	KURU	KURU
28	0.150	0.560	0.380	0.656	6.20	4.16	2.10	0.656	0.380	0.006	KURU	KURU
29	0.150	0.480	0.420	0.656	-----	3.80	1.90	0.656	0.330	0.006	KURU	KURU
30	0.150	0.480	0.420	0.656	-----	3.92	1.70	0.656	0.330	KURU	KURU	KURU
31	0.150	-----	0.420	0.656	-----	5.24	-----	0.656	-----	KURU	KURU	-----
Maks.	0.150	0.608	0.656	1.12	9.60	11.0	4.40	1.70	0.656	0.330	0.020	KURU
Min.	0.034	0.150	0.330	0.420	0.380	3.60	1.70	0.608	0.330	KURU	KURU	KURU
Ortalama	0.101	0.405	0.438	0.590	3.23	5.84	2.58	0.970	0.481	0.106	KURU	KURU
LT/SN/Km2	0.135	0.545	0.590	0.794	4.35	7.87	3.47	1.31	0.647	0.142	0.000	0.000
AKIM mm.	0.363	1.41	1.58	2.13	10.5	21.1	9.00	3.50	1.68	0.382	0.000	0.000
MİL. M3	0.270	1.05	1.17	1.58	7.81	15.7	6.69	2.60	1.25	0.284	0.000	0.000

SU YILI (2006) YILLIK TOPLAM AKIM 38.40 MİLYON M3 52 MM. 1.6 LT/SN/Km2

11. Akarçay Havzasi

D11A020 AKAR Ç. AKDEĞİRMEN

YERİ : **ISPARTA-AFYON-UŞAK YOLUNA TAKİBEN UŞAK İSTİKAMETİNDEN 500 M SONRA SAĞA AKDEĞİRMEN KÖYÜ YOLUNA SAPILILIR. 1.5 KM SONRA AKDEĞIRMEN KÖYÜNE VARILIR. İSTASYON NACAK DERESİ ÜZERİNDEKİ KÖPRÜNÜN 250 M ALTINDA TESİS EDİLMİŞTİR. HARİTA PAFTA NO: K24-A3**
30°13'37" Doğu - 38°48'44" Kuzey

YAĞIŞ ALANI : **203,30 km2** **YAKLAŞIK KOT : 1089 m**

GÖZLEM SÜRESİ : **01.10.1979 - 30.09.2006**

ORTALAMA AKIMLAR : **Gözlem süresinde 0.903 m3/sn. (26 Yıllık) 2006 Su yılında 0.827 m3/sn.**

ANLIK EN ÇOK VE EN AZ AKIMLAR:

2006 Su yılında anlık ençok akım	**:**	**4.81**	**m3/sn**	**14.03.2006**
2006 Su yılında anlık enaz akım	**:**	**0.000**	**m3/sn**	**06.09.2006**
Gözlem süresinde anlık ençok akım	**:**	**15.5**	**m3/sn**	**28.03.1980**
Gözlem süresinde anlık enaz akım	**:**	**0.000**	**m3/sn**	**31.08.1989**

6. Anahtar Eğrisi (Seviyeler cm olarak)

Seviye	Akım	Seviye	Akım	Seviye	Akım	Seviye	Akım
7	0.012	46	1.2	80	2.7	190	6.5
10	0.048	52	1.5	90	3.0	200	6.7
13	0.105	60	1.8	120	4.3	210	7.0
20	0.280	66	2.1	150	5.4	220	7.3
40	0.980	72	2.4	180	6.2	230	7.6

Akımlar 01 Ekim 2005 'den 30 Eylül 2006' a kadar m3/sn olarak

Gün	Ekim	Kasım	Aralık	Ocak	Şubat	Mart	Nisan	Mayıs	Haziran	Temmuz	Ağustos	Eylül
01	0.078	0.095	0.220	0.340	0.855	4.05	2.74	1.09	0.550	0.155	0.019	0.078
02	0.078	0.095	0.220	0.320	0.855	4.05	2.53	1.20	0.500	0.135	0.019	0.095
03	0.078	0.135	0.220	0.320	0.890	3.97	2.40	1.25	0.420	0.180	0.029	0.095
04	0.078	0.220	0.220	0.295	0.890	3.97	2.22	1.37	0.420	0.180	0.019	0.095
05	0.058	0.220	0.220	0.420	0.890	3.93	2.19	1.57	0.395	0.155	0.029	0.135
06	0.029	0.200	0.220	0.295	0.950	3.89	2.02	1.47	0.365	0.155	0.029	KURU
07	0.029	0.180	0.220	0.580	1.13	3.89	2.06	1.33	0.365	0.135	0.029	KURU
08	0.029	0.180	0.220	0.550	1.09	4.13	2.13	1.99	0.365	0.135	0.042	KURU
09	0.029	0.180	0.220	0.500	1.05	3.61	2.10	2.50	0.340	0.135	0.019	KURU
10	0.029	0.180	0.200	0.550	1.05	3.09	1.85	1.67	0.340	0.135	0.042	KURU
11	0.029	0.180	0.200	0.500	2.45	2.84	1.83	1.47	0.365	0.135	0.058	KURU
12	0.029	0.180	0.200	0.470	3.81	2.74	1.78	1.25	0.365	0.135	0.078	KURU
13	0.042	0.180	0.200	0.470	2.45	3.45	1.71	1.17	0.365	0.135	0.095	KURU
14	0.042	0.180	0.200	0.420	1.99	4.81	1.90	1.20	0.365	0.135	0.078	KURU
15	0.042	0.180	0.220	0.420	1.80	3.81	3.05	1.03	0.365	0.135	0.095	KURU
16	0.058	0.180	0.220	0.395	1.64	3.05	2.22	1.44	0.365	0.135	0.135	KURU
17	0.078	0.180	0.245	0.420	1.54	2.84	1.80	1.37	0.320	0.095	0.135	KURU
18	0.078	0.180	0.245	0.420	2.06	2.60	1.60	1.09	0.295	0.029	0.135	KURU
19	0.078	0.180	0.320	0.470	2.22	2.58	1.54	1.00	0.295	0.029	0.135	KURU
20	0.078	0.200	0.340	1.64	2.70	2.25	1.47	0.975	0.295	0.029	0.120	KURU
21	0.078	0.220	0.295	1.05	2.60	2.22	1.37	0.920	0.295	0.029	0.135	KURU
22	0.078	0.220	0.245	1.09	2.60	2.34	1.44	0.820	0.270	0.029	0.135	KURU
23	0.078	0.200	0.270	1.05	2.55	2.88	1.51	0.790	0.270	0.029	0.135	KURU
24	0.078	0.220	0.270	0.950	3.09	3.49	1.44	0.760	0.270	0.042	0.120	KURU
25	0.078	0.200	0.245	0.920	4.69	3.33	1.29	0.730	0.270	0.029	0.135	KURU
26	0.078	0.340	0.245	0.975	4.33	3.02	1.23	0.700	0.270	0.029	0.078	KURU
27	0.078	0.340	0.245	0.950	4.57	2.77	1.20	0.700	0.245	0.029	0.029	KURU
28	0.078	0.270	0.295	0.920	3.57	2.55	1.09	0.700	0.220	0.029	0.029	KURU
29	0.078	0.245	0.295	0.890	-----	2.58	1.13	0.650	0.155	0.029	0.042	KURU
30	0.095	0.245	0.295	0.890	-----	2.81	1.17	0.620	0.155	0.019	0.042	KURU
31	0.095	-----	0.295	0.920	-----	3.17	-----	0.620	-----	0.019	0.058	-----
Maks.	0.095	0.340	0.500	1.64	4.69	4.81	3.05	2.50	0.550	0.180	0.135	0.180
Min.	0.029	0.095	0.200	0.295	0.855	2.22	1.09	0.620	0.155	0.019	0.019	KURU
Ortalama	0.063	0.200	0.244	0.658	2.15	3.25	1.80	1.14	0.329	0.090	0.073	0.017
LT/SN/Km2	0.311	0.985	1.20	3.24	10.6	16.0	8.86	5.62	1.62	0.445	0.361	0.082
AKIM mm.	0.833	2.55	3.22	8.67	25.6	42.8	23.0	15.1	4.20	1.19	0.968	0.212
MİL. M3	0.169	0.519	0.654	1.76	5.21	8.70	4.67	3.06	0.853	0.242	0.197	0.043

SU YILI (2006) YILLIK TOPLAM AKIM 26.08 MİLYON M3 128 MM. 4.1 LT/SN/Km2

11. Akarçay Havzasi

D11A021 ÇAY D. ÇAY

YERİ : **ÇAY KAZASINDAN YALVAÇ YARIKKAYA KÖMÜR OCAKLARINA GİDENYOLUN 4 KM İLERİSİNDEDİR. 31°1'23" Doğu - 38°32'50" Kuzey**

YAĞIŞ ALANI : **62,50 km2** **YAKLAŞIK KOT : 1187 m**

GÖZLEM SÜRESİ : **01.10.1985 - 30.09.2006**

ORTALAMA AKIMLAR : **Gözlem süresinde 0.689 m3/sn. (21 Yıllık) 2006 Su yılında 0.342 m3/sn.**

ANLIK EN ÇOK VE EN AZ AKIMLAR:

2006 Su yılında anlık ençok akım	**:**	**4.20**	**m3/sn**	**02.05.2006**
2006 Su yılında anlık enaz akım	**:**	**0.000**	**m3/sn**	**12.01.2006**
Gözlem süresinde anlık ençok akım	**:**	**27.0**	**m3/sn**	**13.06.1997**
Gözlem süresinde anlık enaz akım	**:**	**0.000**	**m3/sn**	**01.04.1986**

6. Anahtar Eğrisi (Seviyeler cm olarak)

Seviye	Akım	Seviye	Akım	Seviye	Akım	Seviye	Akım
1	0.000	11	0.000	21	0.005	51	2.6
3	0.000	13	0.000	23	0.016	61	5.4
5	0.000	15	0.000	25	0.029	71	9.6
7	0.000	17	0.000	31	0.140	81	14.0
9	0.000	19	0.000	41	0.840	91	18.2

Akımlar 01 Ekim 2005 'den 30 Eylül 2006' a kadar m3/sn olarak

Gün	Ekim	Kasım	Aralık	Ocak	Şubat	Mart	Nisan	Mayıs	Haziran	Temmuz	Ağustos	Eylül
01	0.001	0.001	0.013	0.004	0.002	0.250	2.12	1.86	0.120	0.013	0.004	0.001
02	0.001	0.001	0.013	0.004	0.002	0.250	1.86	4.20	0.092	0.013	0.002	0.001
03	0.001	0.001	0.013	0.004	0.002	0.250	1.29	2.64	0.092	0.013	0.002	0.001
04	0.001	0.001	0.013	0.004	0.002	0.215	1.86	3.16	0.068	0.013	0.002	0.001
05	0.001	0.001	0.009	0.004	0.002	0.180	1.86	3.42	0.068	0.013	0.002	0.001
06	0.001	0.004	0.009	0.004	0.002	0.180	1.29	2.64	0.068	0.009	0.002	0.001
07	0.001	0.004	0.004	0.004	0.092	0.180	0.980	2.64	0.050	0.009	0.001	0.001
08	0.001	0.004	0.006	0.004	0.250	0.180	0.980	2.90	0.050	0.009	0.001	0.001
09	0.001	0.004	0.006	0.004	0.250	0.092	2.12	2.12	0.050	0.009	0.001	0.001
10	0.001	0.004	0.006	0.004	0.250	0.092	2.90	1.60	0.050	0.009	0.001	0.001
11	0.001	0.004	0.006	0.001	0.325	0.068	2.38	1.60	0.068	0.009	0.001	0.001
12	0.001	0.004	0.006	KURU	0.520	0.068	2.38	1.29	0.050	0.009	0.002	0.001
13	0.001	0.004	0.006	KURU	0.325	0.092	2.12	1.60	0.050	0.006	0.001	0.001
14	0.001	0.004	0.004	0.004	0.325	0.120	3.16	0.980	0.050	0.006	0.001	0.001
15	0.001	0.004	0.006	0.006	0.325	0.092	3.68	0.810	0.040	0.006	0.001	0.001
16	0.001	0.004	0.004	0.004	0.325	0.068	3.16	0.640	0.040	0.006	0.001	0.001
17	0.001	0.006	0.004	0.002	0.250	0.068	2.38	0.640	0.027	0.006	0.001	0.001
18	0.001	0.040	0.004	0.001	0.009	0.092	1.29	0.520	0.027	0.006	0.001	0.001
19	0.001	0.215	0.006	KURU	0.006	0.092	2.12	0.520	0.027	0.006	0.001	0.001
20	0.001	0.050	0.004	0.002	0.006	0.092	1.60	0.400	0.020	0.006	0.001	0.001
21	0.001	0.020	0.004	0.004	0.009	0.215	0.980	0.400	0.020	0.006	0.001	0.001
22	0.001	0.009	0.006	0.004	0.013	0.810	2.38	0.400	0.020	0.006	0.001	0.001
23	0.001	0.009	0.006	0.006	0.027	2.90	3.42	0.400	0.020	0.004	0.001	0.001
24	0.001	0.009	0.006	0.006	0.040	3.16	1.86	0.400	0.013	0.004	0.001	0.001
25	0.001	0.009	0.006	0.009	0.068	2.64	0.980	0.325	0.013	0.004	0.001	0.001
26	0.001	0.009	0.006	0.002	0.120	2.12	0.640	0.250	0.020	0.004	0.001	0.001
27	0.001	0.020	0.002	0.002	0.120	1.86	0.640	0.250	0.020	0.004	0.001	0.001
28	0.001	0.027	0.004	0.002	0.120	1.60	0.640	0.215	0.020	0.002	0.001	0.001
29	0.001	0.020	0.004	0.002	-----	1.60	0.640	0.180	0.020	0.002	0.001	0.001
30	0.001	0.020	0.004	0.002	-----	2.12	0.810	0.180	0.020	0.004	0.001	0.001
31	0.001	-----	0.004	0.002	-----	3.16	-----	0.120	-----	0.004	0.001	-----
Maks.	0.001	0.215	0.013	0.009	0.520	3.16	3.68	4.20	0.120	0.013	0.004	0.001
Min.	0.001	0.001	0.002	KURU	0.002	0.068	0.640	0.120	0.013	0.002	0.001	0.001
Ortalama	0.001	0.017	0.006	0.003	0.135	0.803	1.82	1.27	0.043	0.007	0.001	0.001
LT/SN/Km2	0.016	0.273	0.100	0.052	2.16	12.9	29.1	20.3	0.690	0.114	0.021	0.016
AKIM mm.	0.043	0.708	0.268	0.140	5.24	34.4	75.4	54.3	1.79	0.304	0.055	0.041
MİL. M3	0.003	0.044	0.017	0.009	0.327	2.15	4.71	3.40	0.112	0.019	0.003	0.003

SU YILI (2006) YILLIK TOPLAM AKIM 10.80 MİLYON M3 173 MM. 5.5 LT/SN/Km2

11. Akarçay Havzasi

D11A022 DEGİRMEN D. ÖZBURUN

YERİ : **AFYON-ÇAY-BOLVADİN YOLUNA TAKİBEN DIŞLI KASABASI YOLUNA SAPILIR. KASABANIN İÇERİSİNDEN ÖZBURUN YOLUNA SAPILARAK ÖZBURUNA VARLIR. ÖZBURUN ÇIKIŞINDAKİ KÖPRÜDEDİR. HARİTA PAFTA NO: K25-A4**

30°58'53" Doğu - 38°50'0" Kuzey

YAĞIŞ ALANI : **59,00 km2** **YAKLAŞIK KOT : 1160 m**

GÖZLEM SÜRESİ : **15.07.1991 - 30.09.2006**

ORTALAMA AKIMLAR : **Gözlem süresinde 0.087 m3/sn. (10 Yıllık) 2006 Su yılında 0.028 m3/sn.**

ANLIK EN ÇOK VE EN AZ AKIMLAR:

2006 Su yılında anlık ençok akım	:	**0.080**	**m3/sn**	**27.02.2006**
2006 Su yılında anlık enaz akım	:	**0.001**	**m3/sn**	**19.07.2006**
Gözlem süresinde anlık ençok akım	:	**30.6**	**m3/sn**	**22.05.1997**
Gözlem süresinde anlık enaz akım	:	**0.000**	**m3/sn**	**17.10.1998**

2. Anahtar Eğrisi (Seviyeler cm olarak)

Akımlar 01 Ekim 2005 'den 30 Eylül 2006' a kadar m3/sn olarak

Gün	Ekim	Kasım	Aralık	Ocak	Şubat	Mart	Nisan	Mayıs	Haziran	Temmuz	Ağustos	Eylül
01	0.002	0.017	0.035	0.017	0.017	0.080	0.080	0.054	0.008	0.002	0.008	0.017
02	0.002	0.017	0.017	0.017	0.017	0.080	0.080	0.054	0.004	0.002	0.017	0.017
03	0.002	0.017	0.035	0.017	0.017	0.080	0.080	0.080	0.004	0.002	0.017	0.017
04	0.002	0.035	0.035	0.017	0.017	0.080	0.080	0.080	0.004	0.002	0.017	0.035
05	0.002	0.035	0.035	0.017	0.017	0.080	0.080	0.080	0.004	0.002	0.017	0.017
06	0.002	0.035	0.035	0.017	0.017	0.080	0.080	0.080	0.004	0.002	0.017	0.017
07	0.002	0.035	0.017	0.017	0.017	0.080	0.080	0.054	0.004	0.002	0.017	0.017
08	0.002	0.035	0.035	0.017	0.017	0.080	0.080	0.054	0.004	0.002	0.017	0.017
09	0.004	0.035	0.017	0.017	0.017	0.080	0.054	0.054	0.004	0.002	0.017	0.008
10	0.008	0.035	0.017	0.017	0.017	0.080	0.054	0.054	0.004	0.002	0.017	0.004
11	0.017	0.035	0.017	0.017	0.017	0.080	0.054	0.054	0.004	0.002	0.017	0.004
12	0.017	0.035	0.017	0.017	0.017	0.080	0.054	0.054	0.004	0.002	0.017	0.017
13	0.017	0.035	0.017	0.017	0.017	0.080	0.080	0.054	0.004	0.002	0.017	0.017
14	0.017	0.035	0.017	0.017	0.017	0.080	0.080	0.054	0.004	0.002	0.017	0.017
15	0.035	0.035	0.017	0.017	0.017	0.080	0.080	0.035	0.004	0.002	0.017	0.017
16	0.035	0.035	0.017	0.017	0.017	0.080	0.080	0.035	0.004	0.002	0.017	0.017
17	0.017	0.035	0.017	0.017	0.017	0.080	0.054	0.035	0.004	0.002	0.008	0.017
18	0.017	0.035	0.017	0.017	0.017	0.080	0.080	0.035	0.004	0.002	0.008	0.017
19	0.017	0.035	0.017	0.017	0.017	0.080	0.054	0.035	0.004	0.001	0.017	0.008
20	0.017	0.035	0.017	0.017	0.035	0.080	0.054	0.035	0.004	0.001	0.017	0.017
21	0.017	0.035	0.017	0.017	0.035	0.080	0.054	0.035	0.004	0.001	0.017	0.017
22	0.017	0.035	0.017	0.017	0.054	0.080	0.054	0.017	0.004	0.001	0.008	0.017
23	0.017	0.035	0.017	0.017	0.054	0.080	0.054	0.017	0.004	0.001	0.017	0.017
24	0.017	0.035	0.017	0.017	0.080	0.080	0.054	0.017	0.004	0.001	0.017	0.017
25	0.017	0.035	0.017	0.017	0.080	0.080	0.054	0.017	0.004	0.001	0.017	0.017
26	0.017	0.035	0.017	0.017	0.080	0.080	0.080	0.017	0.004	0.001	0.017	0.017
27	0.017	0.035	0.017	0.017	0.080	0.080	0.054	0.017	0.004	0.001	0.008	0.017
28	0.017	0.017	0.017	0.017	0.080	0.080	0.054	0.017	0.004	0.004	0.008	0.017
29	0.017	0.035	0.017	0.017	-----	0.080	0.054	0.017	0.004	0.008	0.004	0.017
30	0.017	0.035	0.017	0.017	-----	0.080	0.054	0.008	0.002	0.008	0.008	0.017
31	0.017	-----	0.017	0.017	-----	0.080	-----	0.008	-----	0.017	0.017	-----
Maks.	0.035	0.035	0.035	0.017	0.080	0.080	0.080	0.080	0.008	0.017	0.017	0.035
Min.	0.002	0.017	0.017	0.017	0.017	0.080	0.054	0.008	0.002	0.001	0.004	0.004
Ortalama	0.014	0.033	0.020	0.017	0.032	0.080	0.066	0.041	0.004	0.003	0.015	0.016
LT/SN/Km2	0.230	0.553	0.347	0.288	0.545	1.36	1.12	0.687	0.069	0.045	0.247	0.273
AKIM mm.	0.617	1.43	0.930	0.772	1.32	3.63	2.91	1.84	0.179	0.120	0.660	0.709
MİL. M3	0.036	0.084	0.055	0.046	0.078	0.214	0.171	0.109	0.011	0.007	0.039	0.042

SU YILI (2006) YILLIK TOPLAM AKIM 0.89 MİLYON M3 15 MM. 0.5 LT/SN/Km2

11. Akarçay Havzasi

D11A023 EBER G. GİRİŞ

YERİ : **ÇAY-BOLVADİN ASFALT YOLUNU TAKİBEN DEVELİ KÖPRÜSÜNE GELİNİR. KÖPRÜNÜN BİTİMİNDEN SOLA GİDEN TOPRAK YOLDAN İKİ KM GİDİLDİKTEN SONRA KÖPRÜNÜN SOL SAHİLİNDEDİR. 31°1'24" Doğu - 38°39'49" Kuzey**

YAĞIŞ ALANI : **4160,40 km2** **YAKLAŞIK KOT : 970 m**

GÖZLEM SÜRESİ : **01.10.1998 - 30.09.2006**

ORTALAMA AKIMLAR : **Gözlem süresinde 2.655 m3/sn. (5 Yıllık) 2006 Su yılında 1.853 m3/sn.**

ANLIK EN ÇOK VE EN AZ AKIMLAR:

2006 Su yılında anlık ençok akım	**:**	**16.5**	**m3/sn**	**15.03.2006**
2006 Su yılında anlık enaz akım	**:**	**0.000**	**m3/sn**	**30.06.2006**
Gözlem süresinde anlık ençok akım	**:**	**35.9**	**m3/sn**	**26.02.1999**
Gözlem süresinde anlık enaz akım	**:**	**0.000**	**m3/sn**	**31.07.2003**

1. Anahtar Eğrisi (Seviyeler cm olarak)

Seviye	Akım	Seviye	Akım	Seviye	Akım	Seviye	Akım
10	0.030	25	0.340	110	11.0	210	36.5
12	0.050	35	0.790	130	15.5	230	45.0
15	0.094	50	1.9	150	20.0	240	48.0
17	0.128	70	4.1	170	25.5	250	52.0
19	0.170	90	7.2	190	30.5	260	56.0

Akımlar 01 Ekim 2005 'den 30 Eylül 2006' a kadar m3/sn olarak

Gün	Ekim	Kasım	Aralık	Ocak	Şubat	Mart	Nisan	Mayıs	Haziran	Temmuz	Ağustos	Eylül
01	0.021	0.340	0.380	0.976	2.70	11.2	12.0	0.852	0.145	KURU	KURU	0.030
02	0.021	0.340	0.380	0.540	2.70	9.20	8.10	0.852	0.145	KURU	KURU	0.030
03	0.021	0.380	0.340	0.740	2.70	7.74	7.56	0.852	0.063	KURU	0.015	0.030
04	0.021	0.500	0.311	0.500	2.70	9.40	7.20	0.740	0.063	KURU	0.015	0.075
05	0.021	0.690	0.282	0.460	2.70	14.5	6.86	0.740	0.063	KURU	0.021	0.075
06	0.021	0.852	0.282	0.500	2.70	7.92	7.74	0.740	0.063	KURU	0.021	0.075
07	0.030	0.640	0.282	0.500	2.70	7.92	7.56	0.640	0.063	KURU	0.030	0.094
08	0.039	0.590	0.282	0.500	2.80	6.69	7.03	0.640	0.063	KURU	0.050	0.128
09	0.021	0.540	0.252	0.500	3.14	7.03	6.52	0.640	0.063	KURU	0.108	0.145
10	0.021	0.460	0.252	0.740	3.26	7.38	6.69	0.590	0.063	KURU	0.108	0.223
11	0.021	0.460	0.252	1.18	3.26	6.52	5.67	0.590	0.050	KURU	0.021	0.223
12	0.021	0.460	0.282	0.790	3.86	6.52	5.22	0.590	0.050	KURU	0.021	0.223
13	0.030	0.460	0.282	0.540	4.10	11.8	4.38	0.540	0.063	KURU	0.021	0.282
14	0.030	0.420	0.282	0.500	5.22	12.0	2.60	0.500	0.063	KURU	0.021	0.252
15	0.030	0.420	0.252	0.540	4.66	16.5	1.10	0.500	0.075	KURU	0.021	0.282
16	0.030	0.420	0.282	0.540	3.26	16.3	0.914	0.460	0.128	KURU	0.021	0.282
17	0.030	0.340	0.282	1.66	4.10	11.8	0.914	0.460	0.145	KURU	0.021	0.420
18	0.030	0.282	0.282	2.50	6.52	8.64	0.852	0.311	0.063	KURU	0.021	0.380
19	0.030	0.223	0.282	1.66	3.14	6.18	1.26	0.311	0.063	KURU	0.021	0.380
20	0.030	0.223	0.311	0.852	3.74	5.84	2.10	0.252	0.063	KURU	0.021	0.540
21	0.030	0.282	0.340	0.914	5.50	5.08	2.40	0.252	0.063	KURU	0.021	0.170
22	0.030	0.340	0.340	1.18	5.67	7.56	2.60	0.223	0.063	KURU	0.021	0.128
23	0.030	0.380	0.420	2.80	5.67	12.4	3.14	0.223	0.063	KURU	0.021	0.145
24	0.030	0.340	0.460	2.70	5.67	13.0	4.80	0.194	0.063	KURU	0.021	0.194
25	0.030	0.311	0.540	2.70	5.50	14.3	5.08	0.194	0.063	KURU	0.021	0.340
26	0.030	0.311	0.640	2.70	5.50	14.3	4.52	0.194	0.063	KURU	0.021	0.500
27	0.030	0.311	0.790	2.70	14.8	13.5	3.50	0.170	0.063	KURU	0.021	1.26
28	0.030	0.380	0.852	2.70	12.6	12.4	2.50	0.170	0.021	KURU	0.030	1.04
29	0.030	0.420	0.976	2.70	-----	10.6	1.18	0.170	KURU	KURU	0.039	0.852
30	0.030	0.420	1.26	2.70	-----	10.4	0.914	0.170	KURU	KURU	0.075	0.740
31	0.030	-----	1.04	2.70	-----	11.4	-----	0.145	-----	KURU	0.039	-----
Maks.	0.039	0.852	1.26	2.80	14.8	16.5	12.0	0.852	0.145	KURU	0.108	1.26
Min.	0.021	0.223	0.252	0.460	2.70	0.852	0.852	0.145	KURU	KURU	KURU	0.030
Ortalama	0.027	0.418	0.435	1.39	4.67	10.2	4.43	0.449	0.067	KURU	0.029	0.318
LT/SN/Km2	0.007	0.100	0.105	0.335	1.12	2.45	1.06	0.108	0.016	0.000	0.007	0.076
AKIM mm.	0.018	0.260	0.280	0.897	2.72	6.56	2.76	0.289	0.042	0.000	0.019	0.198
MİL. M3	0.073	1.08	1.17	3.73	11.3	27.3	11.5	1.20	0.174	0.000	0.078	0.824

SU YILI (2006) YILLIK TOPLAM AKIM 58.43 MİLYON M3 14 MM. 0.4 LT/SN/Km2

12

SAKARYA HAVZASI

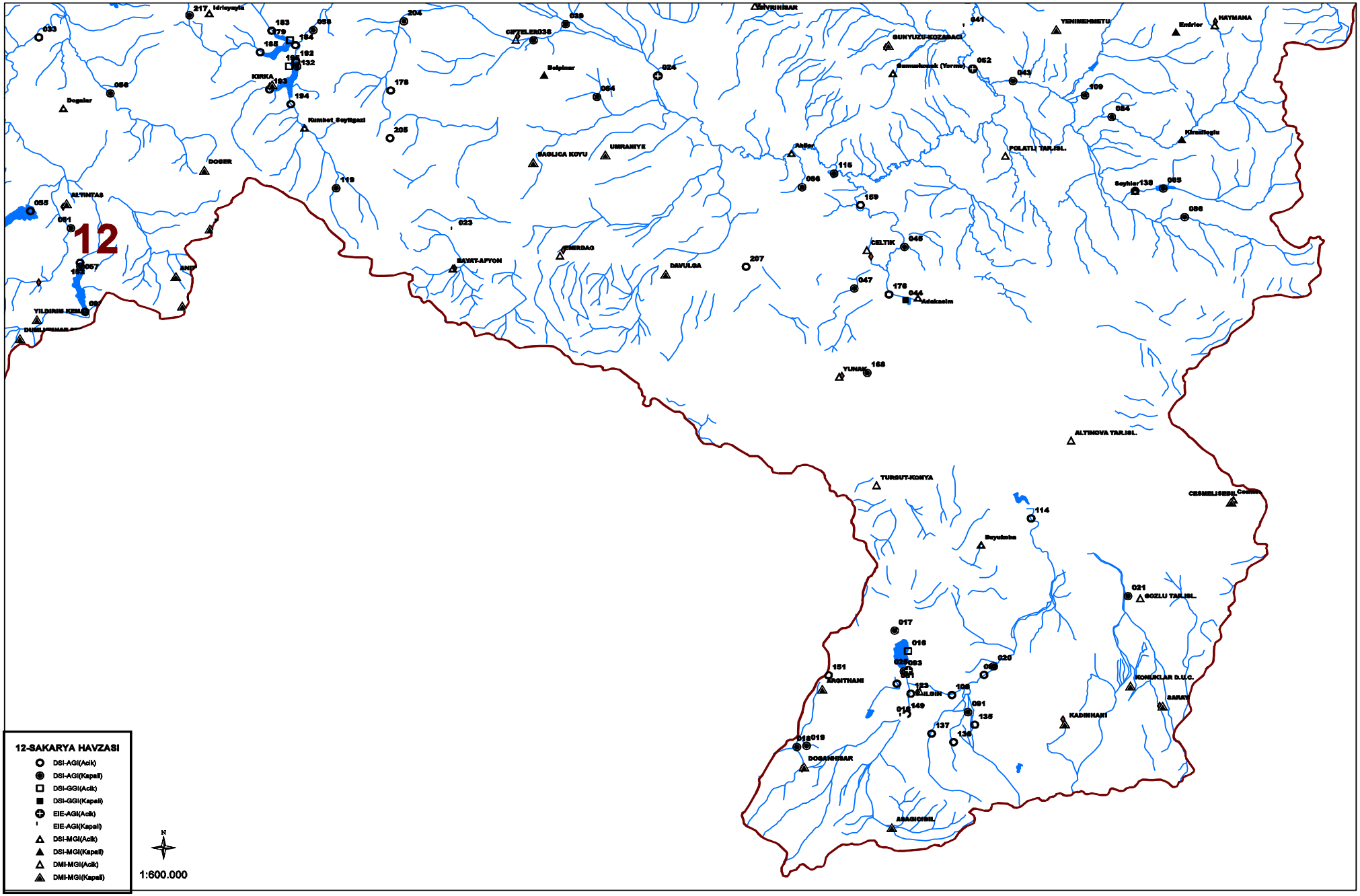
12
12-SAKARYA HAVZASI
DSI-AGI(Acik)
DSI-AGI(Kapali)
DSI-GGI(Acik)
DSI-GGI(Kapali)
EIE-AGI(Acik)
EIE-AGI(Kapali)
DSI-MGI(Acik)
DSI-MGI(Kapali)
DMI-MGI(Acik)
DMI-MGI(Kapali)
N
1:600.000
Idriseyli
KIRKA
Kumbet_Seytgazi
Doganlar
DOGER
ALTINTAS
YILDIRIM KEMAL
BAGLICA KOYU
UMRANIYE
BAYAT-AFYON
EMIRDAG
DAVULGA
SUVMINBAR
GUNYUZU-KOZABACI
Samanbayak (Yorma)
POLATLI TAR.ISL.
YENIMEHMETLI
HAYMANA
Kirazlioglu
CELTIK
Adakasim
YUNAK
ALTINOVA TAR.ISL.
TURSUT-KONYA
CESMELISEBIL
Bayalanbe
GOZLU TAR.ISL.
KONUKLAR D.U.C.
RARAV
KADINHANI
INSITHANI
DOGANHISAR
ASAGICIBIL

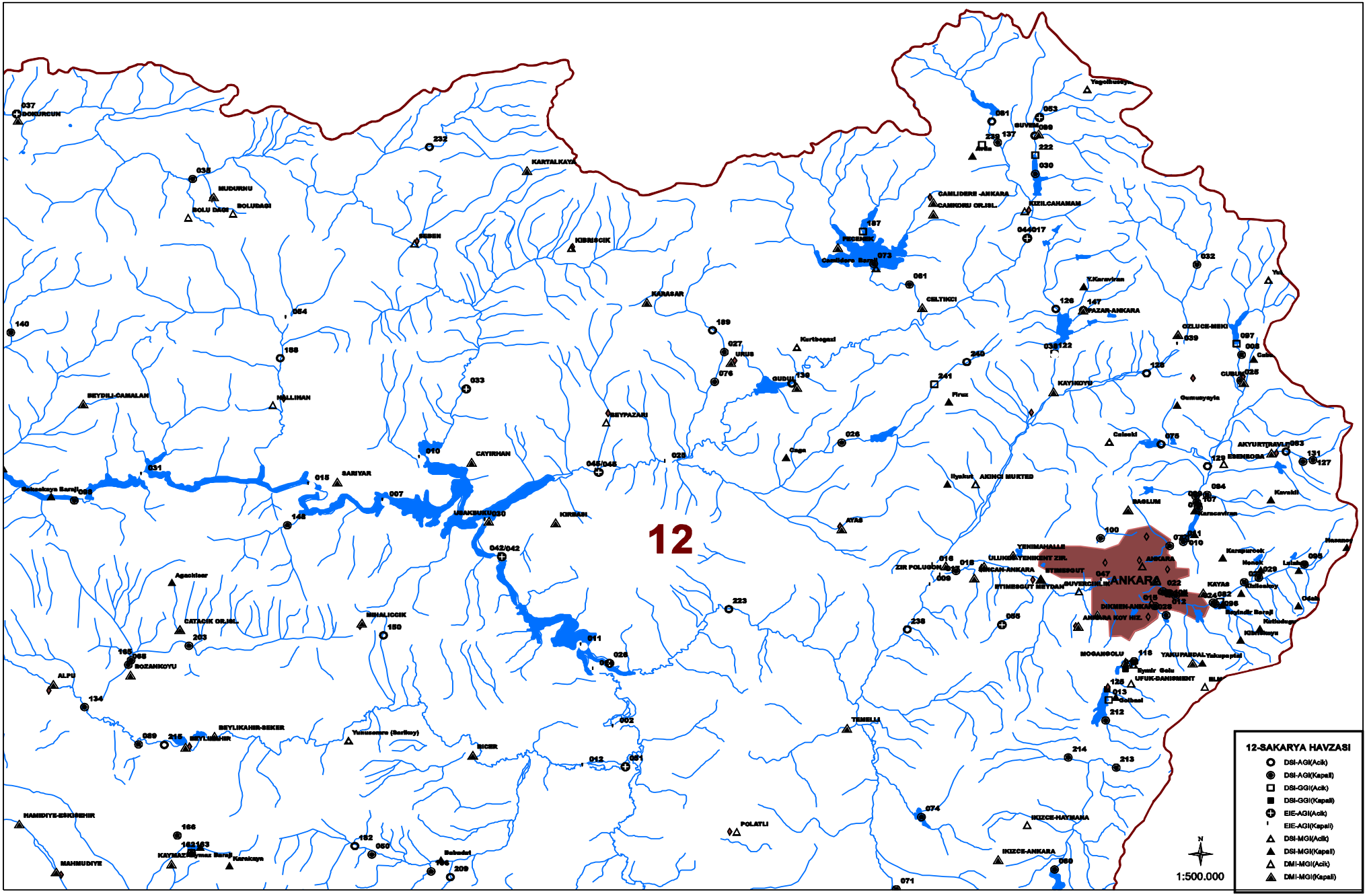
12
ANKARA
12-SAKARYA HAVZASI
DSI-AGI(Acik)
DSI-AGI(Kapali)
DSI-GGI(Acik)
DSI-GGI(Kapali)
EIE-AGI(Acik)
EIE-AGI(Kapali)
DSI-MGI(Acik)
DSI-MGI(Kapali)
DMI-MGI(Acik)
DMI-MGI(Kapali)
N
1:500.000

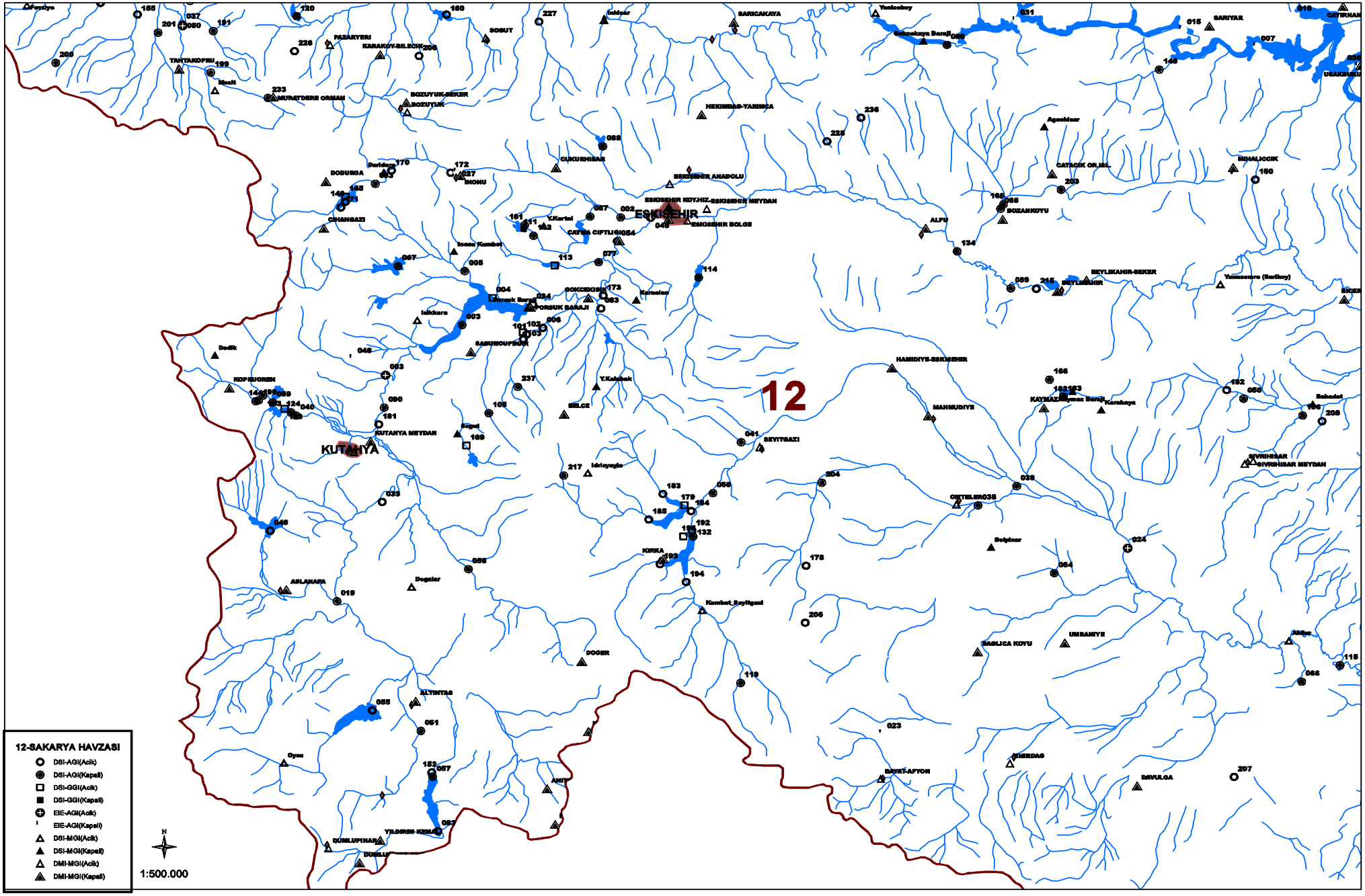
12
ESKISEHIR
KUTAHYA
12-SAKARYA HAVZASI
DSI-AGI(Acik)
DSI-AGI(Kapali)
DSI-GGI(Acik)
DSI-GGI(Kapali)
EIE-AGI(Acik)
EIE-AGI(Kapali)
DSI-MGI(Acik)
DSI-MGI(Kapali)
DMI-MGI(Acik)
DMI-MGI(Kapali)
N
1:500.000

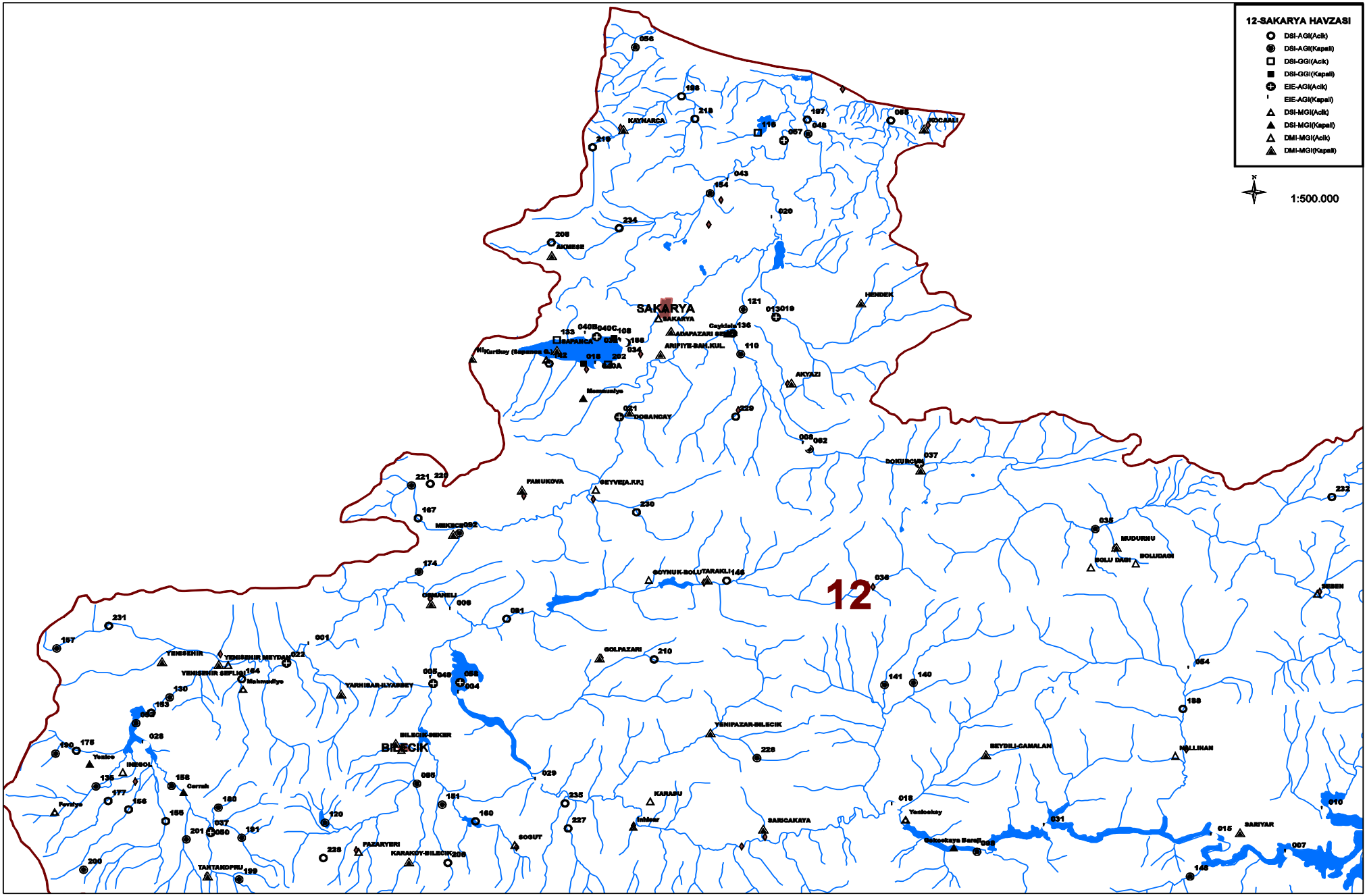
12-SAKARYA HAVZASI
DSI-AGI(Acik)
DSI-AGI(Kapali)
DSI-GGI(Acik)
DSI-GGI(Kapali)
EIE-AGI(Acik)
EIE-AGI(Kapali)
DSI-MGI(Acik)
DSI-MGI(Kapali)
DMI-MGI(Acik)
DMI-MGI(Kapali)
N
1:500.000
12
SAKARYA
BILECIK
KAYNARCA
KOCAALI
AKOBSE
HENDEK
ADAPAZARI
ARIFIYE-BAH.KUL.
AKYAZI
DOBANCAY
PAMUKOVA
SEYVE(A.KU)
MEKECE
MUDURNU
BOLU DAGI
BOLUDAGI
GOYNUK-BOLUTARAKLI
GOLPAZARI
YENISEHIR
YENISEHIR MEYDAN
YENISEHIR SEFLIKI
YARHISAR-ILYASBEY
YENIPAZAR-BILECIK
SEYDILI-CAMALAN
HOLLIHAN
KARASU
SARICAKAYA
SOGUT
PAZARYERI
KARAKOY-BILECIK
TARTANDPINU
SARIYAR

12. Sakarya Havzasi

D12A017 KIZILCAHAMAM DERESİ MANDIRA

YERİ : **KIZILCAHAMAM ÇELTİKÇİ YOL AYRIMININ 3.KM SİNDE SAĞ SAHİLDEDİR**
32°38'58" Doğu - 40°25'57" Kuzey

YAĞIŞ ALANI : **907.50 km2** **YAKLAŞIK KOT : 903 m**

GÖZLEM SÜRESİ : **01.04.1959 – 30.09.2006**

ORTALAMA AKIMLAR : **Gözlem süresinde 5.019 m3/sn. (43 Yıllık) 2006 Su yılında 0.866 m3/sn.**

ANLIK EN ÇOK VE EN AZ AKIMLAR:

2006 Su yılında anlık ençok akım	**:**	**8.08**	**m3/sn**	**03.03.2006**
2006 Su yılında anlık enaz akım	**:**	**0.260**	**m3/sn**	**25.05.2006**
Gözlem süresinde anlık ençok akım	**:**	**960.**	**m3/sn**	**12.03.1968**
Gözlem süresinde anlık enaz akım	**:**	**0.050**	**m3/sn**	**23.08.1961**

Akımlar 01 Ekim 2005 'den 30 Eylül 2006' a kadar m3/sn olarak

Gün	Ekim	Kasım	Aralık	Ocak	Şubat	Mart	Nisan	Mayıs	Haziran	Temmuz	Ağustos	Eylül
01	0.720	0.570	0.570	0.570	0.570	3.16	2.50	0.720	0.420	0.420	0.260	0.260
02	0.720	0.570	0.570	0.570	0.570	4.24	2.50	0.570	0.420	0.420	0.260	0.260
03	0.880	0.570	0.570	0.570	0.570	6.28	2.10	0.570	0.420	0.420	0.260	0.260
04	0.880	0.570	0.570	0.570	0.570	5.02	2.10	0.570	0.420	0.420	0.260	0.260
05	0.880	0.570	0.570	0.570	0.570	3.52	1.85	0.570	0.420	0.420	0.260	0.260
06	0.880	0.570	0.570	0.570	0.570	3.52	1.55	0.570	0.420	0.420	0.260	0.260
07	0.720	0.570	0.570	0.570	0.570	3.52	1.55	0.720	0.420	0.420	0.260	0.260
08	0.570	0.570	0.570	0.570	0.570	4.24	1.55	0.720	0.420	0.420	0.260	0.260
09	0.570	0.570	0.570	0.570	0.570	5.02	1.55	0.720	0.420	0.420	0.260	0.260
10	0.570	0.570	0.570	0.570	0.570	4.24	1.55	0.720	0.420	0.420	0.260	0.260
11	0.570	0.880	0.570	0.570	1.15	3.16	0.880	0.720	0.420	0.420	0.260	0.260
12	0.720	0.570	0.570	0.570	1.30	2.80	0.880	0.720	0.420	0.420	0.260	0.260
13	0.570	0.570	0.570	0.570	0.880	3.88	1.15	0.720	0.420	0.420	0.260	0.260
14	0.570	0.570	0.570	0.570	0.720	5.02	1.15	0.720	0.420	0.420	0.260	0.260
15	0.570	0.570	0.570	0.570	0.720	5.86	1.15	0.720	0.570	0.420	0.260	0.260
16	0.570	0.570	0.570	0.570	0.570	4.24	0.880	0.570	0.570	0.420	0.260	0.260
17	0.570	0.570	0.570	0.570	0.720	3.88	0.720	0.570	0.570	0.420	0.260	0.260
18	0.570	0.570	0.570	0.570	0.570	2.80	0.720	0.570	0.420	0.420	0.260	0.260
19	0.720	0.570	0.570	0.570	0.570	2.80	0.720	0.570	0.420	0.420	0.260	0.260
20	0.720	0.720	0.570	0.570	0.720	2.50	0.570	0.570	0.420	0.420	0.260	0.260
21	0.720	0.720	0.570	0.570	1.30	2.10	0.720	0.570	0.420	0.420	0.260	0.260
22	0.570	0.570	0.570	0.570	2.10	2.10	0.570	0.570	0.420	0.420	0.260	0.260
23	0.570	0.570	0.570	0.570	2.50	3.16	0.420	0.420	0.420	0.420	0.260	0.260
24	0.570	0.570	0.570	0.570	2.50	5.02	0.420	0.420	0.420	0.420	0.260	0.260
25	0.570	0.570	0.570	0.570	3.16	4.60	0.420	0.420	0.420	0.420	0.260	0.260
26	0.570	0.570	0.570	0.570	4.60	3.88	0.570	0.260	0.420	0.420	0.260	0.260
27	0.570	0.570	0.570	0.570	4.24	3.16	0.570	0.420	0.420	0.260	0.260	0.260
28	0.570	0.570	0.570	0.570	3.16	2.80	0.570	0.420	0.420	0.260	0.260	0.260
29	0.570	0.570	0.570	0.570	-----	2.50	0.570	0.420	0.420	0.260	0.260	0.260
30	0.570	0.570	0.570	0.570	-----	2.50	0.570	0.420	0.420	0.260	0.260	0.260
31	0.570	-----	0.570	0.570	-----	2.50	-----	0.420	-----	0.260	0.260	-----
Maks.	1.30	1.15	0.880	1.30	5.86	8.08	2.50	1.55	0.880	1.30	0.260	0.420
Min.	0.570	0.570	0.570	0.420	0.420	2.10	0.420	0.260	0.260	0.260	0.260	0.260
Ortalama	0.644	0.590	0.570	0.570	1.33	3.68	1.10	0.570	0.435	0.394	0.260	0.260
LT/SN/Km2	0.709	0.651	0.628	0.628	1.46	4.05	1.21	0.628	0.479	0.434	0.287	0.287
AKIM mm.	1.90	1.69	1.68	1.68	3.54	10.9	3.14	1.68	1.24	1.16	0.767	0.743
MİL. M3	1.72	1.53	1.53	1.53	3.21	9.85	2.85	1.53	1.13	1.06	0.696	0.674

SU YILI (2006) YILLIK TOPLAM AKIM 27.31 MİLYON M3 30 MM. 1.0 LT/SN/Km2

12. Sakarya Havzasi

D12A033 PORSUK Ç. PORSUK ÇİFTLIGI

YERİ : **KÜTAHYA-AFYON YOLUNUN 10.KM SİNDEN SAĞA AYRILAN GEDİZYOLUNUN 1.5 KM SİNDEKİ KÖPRÜNÜN MENBAINDADIR.**
30°2'0" Doğu - 39°21'0" Kuzey

YAĞIŞ ALANI : **2432.00 km2** **YAKLAŞIK KOT : 951 m**

GÖZLEM SÜRESİ : **01.12.1960 - 30.09.2006**

ORTALAMA AKIMLAR : **Gözlem süresinde 4.755 m3/sn. (40 Yıllık) 2006 Su yılında 3.535 m3/sn.**

ANLIK EN ÇOK VE EN AZ AKIMLAR:

2006 Su yılında anlık ençok akım	**:**	**42.1**	**m3/sn**	**05.03.2006**
2006 Su yılında anlık enaz akım	**:**	**0.203**	**m3/sn**	**18.08.2006**
Gözlem süresinde anlık ençok akım	**:**	**104.**	**m3/sn**	**25.02.2005**
Gözlem süresinde anlık enaz akım	**:**	**0.097**	**m3/sn**	**22.09.2001**

15. Anahtar Eğrisi (Seviyeler cm olarak)

Seviye	Akım	Seviye	Akım	Seviye	Akım
36	0.200	80	3.4	150	20.5
40	0.275	90	4.9	162	25.8
50	0.638	100	6.4	181	35.0
60	1.0	114	9.2	240	76.9
70	1.8	130	13.0	300	135.

Akımlar 01 Ekim 2005 'den 30 Eylül 2006' a kadar m3/sn olarak

Gün	Ekim	Kasım	Aralık	Ocak	Şubat	Mart	Nisan	Mayıs	Haziran	Temmuz	Ağustos	Eylül
01	0.442	0.545	0.973	1.02	1.49	27.7	7.61	3.69	1.62	0.830	0.477	0.237
02	0.442	0.545	0.878	1.02	1.29	24.9	7.21	3.69	1.49	0.783	0.442	0.306
03	0.442	0.545	0.878	1.02	1.29	25.8	6.41	3.69	1.42	0.783	0.442	0.306
04	0.511	0.688	0.830	1.02	1.36	32.1	6.41	3.69	1.36	0.783	0.408	0.306
05	0.511	0.735	0.830	1.09	1.36	38.6	6.24	3.69	1.29	0.783	0.374	0.306
06	0.511	0.735	0.830	1.15	1.42	25.4	6.08	3.69	1.15	0.783	0.374	0.306
07	0.511	0.735	0.830	1.42	1.42	17.9	5.91	3.69	1.09	0.688	0.374	0.306
08	0.545	0.735	0.830	1.69	1.49	15.3	5.58	3.92	1.09	0.593	0.340	0.306
09	0.545	0.735	0.783	1.77	1.69	15.3	5.58	4.39	1.09	0.545	0.340	0.271
10	0.545	0.735	0.783	1.69	1.77	15.6	5.58	4.39	1.15	0.511	0.340	0.271
11	0.511	0.735	0.783	1.56	2.16	15.3	5.58	4.27	1.15	0.511	0.340	0.271
12	0.545	0.735	0.783	1.56	4.74	14.9	5.41	3.80	1.22	0.511	0.340	0.271
13	0.545	0.735	0.783	1.56	13.8	14.1	4.91	3.80	1.22	0.511	0.340	0.306
14	0.545	0.735	0.783	1.56	11.3	14.9	4.91	3.80	1.22	0.511	0.340	0.306
15	0.545	0.735	0.783	1.42	11.3	19.8	4.91	3.80	1.22	0.511	0.340	0.306
16	0.545	0.735	0.783	1.42	11.3	21.8	5.07	3.69	1.15	0.477	0.340	0.306
17	0.545	0.735	0.830	1.36	10.4	17.9	5.24	3.57	1.15	0.442	0.340	0.306
18	0.545	0.735	0.830	1.29	6.81	16.0	5.24	3.57	1.15	0.442	0.271	0.306
19	0.545	0.735	0.830	1.36	7.82	14.5	4.74	3.46	1.15	0.442	0.237	0.306
20	0.545	0.735	0.830	1.42	15.6	13.8	4.62	3.35	1.02	0.408	0.237	0.340
21	0.545	0.783	0.878	3.35	22.7	12.3	4.39	2.92	1.02	0.374	0.237	0.340
22	0.545	0.830	0.973	2.81	24.5	11.8	4.27	2.59	1.02	0.374	0.237	0.340
23	0.545	0.830	0.925	2.59	21.4	11.3	4.27	2.40	1.02	0.442	0.237	0.408
24	0.545	0.830	0.830	2.40	19.8	11.6	4.39	2.24	0.925	0.442	0.237	0.477
25	0.545	0.830	0.783	2.40	20.9	12.1	4.51	2.09	0.830	0.477	0.237	0.477
26	0.545	0.830	0.783	2.32	29.2	13.0	4.39	1.93	0.783	0.593	0.237	0.477
27	0.545	0.830	1.02	2.01	35.0	12.5	4.39	1.85	0.830	0.545	0.237	0.477
28	0.545	0.925	1.02	1.77	39.3	11.8	3.80	1.77	0.925	0.511	0.237	0.511
29	0.545	0.973	1.02	1.69	-----	11.3	3.57	1.69	0.878	0.511	0.237	0.735
30	0.545	0.973	1.02	1.69	-----	8.62	3.69	1.62	0.830	0.477	0.237	0.593
31	0.545	-----	1.02	1.62	-----	7.61	-----	1.62	-----	0.477	0.237	-----
Maks.	0.545	1.02	1.29	4.16	41.4	42.1	7.61	4.51	1.62	0.830	0.477	2.09
Min.	0.271	0.545	0.688	0.973	1.15	7.61	3.57	1.62	0.783	0.374	0.203	0.237
Ortalama	0.530	0.757	0.862	1.68	11.5	17.0	5.16	3.17	1.12	0.551	0.311	0.359
LT/SN/Km2	0.218	0.311	0.355	0.690	4.74	6.97	2.12	1.30	0.459	0.226	0.128	0.148
AKIM mm.	0.583	0.807	0.950	1.85	11.5	18.7	5.50	3.49	1.19	0.606	0.343	0.383
MİL. M3	1.42	1.96	2.31	4.50	27.9	45.4	13.4	8.50	2.89	1.47	0.833	0.931

SU YILI (2006) YILLIK TOPLAM AKIM 111.51 MİLYON M3 46 MM. 1.5 LT/SN/Km2

12. Sakarya Havzasi

D12A049 KUREYŞLER D. KUREYŞLER

YERİ : **KÜTAHYA GEDİZ YOLUNUN 33.KM SİNDEKİ SARAY KÖYÜNDEN SAĞAAYRILAN HAM YOLUN 4 KM SİNDEKİ KUREYŞLER KÖYÜNÜN 300MT**
29°51'0" Doğu - 39°18'0" Kuzey

YAĞIŞ ALANI : **112.70 km2** **YAKLAŞIK KOT : 1029 m**

GÖZLEM SÜRESİ : **01.06.1963 - 30.09.2006**

ORTALAMA AKIMLAR : **Gözlem süresinde 0.305 m3/sn. (41 Yıllık) 2006 Su yılında 0.154 m3/sn.**

ANLIK EN ÇOK VE EN AZ AKIMLAR:

2006 Su yılında anlık ençok akım	:	**0.911**	**m3/sn**	**20.02.2006**
2006 Su yılında anlık enaz akım	:	**0.016**	**m3/sn**	**24.08.2006**
Gözlem süresinde anlık ençok akım	:	**58.0**	**m3/sn**	**12.03.1968**
Gözlem süresinde anlık enaz akım	:	**0.000**	**m3/sn**	**09.07.2002**

11. Anahtar Eğrisi (Seviyeler cm olarak)

Seviye	Akım	Seviye	Akım	Seviye	Akım	Seviye	Akım
1	0.006	12	0.349	40	2.6	80	7.9
3	0.033	15	0.500	44	3.1	90	9.5
5	0.076	20	0.834	50	3.7	100	11.1
7	0.135	28	1.4	60	5.0	130	16.9
9	0.200	32	1.8	70	6.4	193	30.0

Akımlar 01 Ekim 2005 'den 30 Eylül 2006' a kadar m3/sn olarak

Gün	Ekim	Kasım	Aralık	Ocak	Şubat	Mart	Nisan	Mayıs	Haziran	Temmuz	Ağustos	Eylül
01	0.135	0.135	0.135	0.135	0.135	0.200	0.248	0.200	0.135	0.102	0.076	0.102
02	0.135	0.135	0.135	0.135	0.135	0.200	0.248	0.200	0.135	0.102	0.076	0.102
03	0.135	0.135	0.135	0.135	0.135	0.349	0.248	0.200	0.135	0.102	0.076	0.102
04	0.135	0.135	0.135	0.135	0.135	0.299	0.248	0.200	0.135	0.135	0.076	0.102
05	0.135	0.135	0.135	0.160	0.135	0.248	0.248	0.200	0.135	0.102	0.076	0.102
06	0.135	0.135	0.135	0.160	0.160	0.200	0.200	0.200	0.135	0.135	0.076	0.102
07	0.135	0.135	0.135	0.160	0.160	0.200	0.248	0.200	0.135	0.135	0.076	0.102
08	0.135	0.135	0.135	0.160	0.160	0.248	0.248	0.248	0.135	0.102	0.076	0.102
09	0.135	0.135	0.135	0.135	0.160	0.200	0.248	0.248	0.135	0.102	0.102	0.102
10	0.135	0.135	0.135	0.135	0.200	0.200	0.248	0.200	0.135	0.102	0.076	0.135
11	0.135	0.135	0.135	0.135	0.299	0.200	0.248	0.200	0.200	0.102	0.076	0.102
12	0.135	0.135	0.135	0.135	0.299	0.200	0.200	0.200	0.200	0.102	0.076	0.135
13	0.135	0.135	0.135	0.135	0.248	0.200	0.200	0.200	0.200	0.102	0.076	0.102
14	0.135	0.135	0.135	0.135	0.248	0.200	0.200	0.200	0.200	0.102	0.076	0.102
15	0.135	0.135	0.135	0.135	0.200	0.200	0.200	0.200	0.200	0.102	0.102	0.102
16	0.135	0.135	0.135	0.135	0.200	0.200	0.200	0.200	0.160	0.102	0.102	0.102
17	0.135	0.135	0.135	0.135	0.200	0.200	0.200	0.200	0.160	0.102	0.102	0.135
18	0.135	0.135	0.135	0.135	0.200	0.200	0.200	0.200	0.160	0.102	0.102	0.102
19	0.135	0.135	0.135	0.135	0.248	0.200	0.200	0.200	0.135	0.102	0.102	0.135
20	0.135	0.135	0.135	0.135	0.349	0.200	0.200	0.200	0.102	0.102	0.102	0.135
21	0.135	0.135	0.135	0.135	0.349	0.200	0.200	0.200	0.102	0.102	0.102	0.135
22	0.135	0.135	0.135	0.135	0.349	0.200	0.200	0.200	0.102	0.102	0.102	0.135
23	0.135	0.135	0.135	0.135	0.248	0.200	0.248	0.200	0.102	0.102	0.076	0.135
24	0.135	0.135	0.135	0.135	0.248	0.248	0.200	0.160	0.102	0.102	0.102	0.135
25	0.135	0.135	0.135	0.135	0.248	0.248	0.200	0.160	0.102	0.102	0.102	0.135
26	0.135	0.200	0.135	0.135	0.248	0.248	0.200	0.160	0.102	0.102	0.102	0.135
27	0.135	0.160	0.135	0.135	0.248	0.248	0.200	0.160	0.102	0.102	0.102	0.135
28	0.135	0.160	0.135	0.135	0.248	0.248	0.200	0.160	0.102	0.102	0.102	0.135
29	0.135	0.160	0.135	0.135	-----	0.248	0.200	0.160	0.102	0.102	0.102	0.160
30	0.135	0.135	0.135	0.135	-----	0.248	0.200	0.160	0.102	0.102	0.102	0.160
31	0.135	-----	0.135	0.135	-----	0.248	-----	0.160	-----	0.076	0.102	-----
Maks.	0.135	0.248	0.135	0.160	0.911	0.448	0.299	0.299	0.200	0.200	0.395	0.160
Min.	0.135	0.135	0.135	0.135	0.033	0.160	0.160	0.135	0.052	0.033	0.016	0.076
Ortalama	0.135	0.140	0.135	0.138	0.221	0.223	0.218	0.193	0.136	0.104	0.090	0.120
LT/SN/Km2	1.20	1.24	1.20	1.23	1.96	1.98	1.93	1.71	1.21	0.926	0.801	1.07
AKIM mm.	3.21	3.21	3.21	3.29	4.75	5.31	5.00	4.58	3.13	2.48	2.15	2.76
MİL. M3	0.362	0.362	0.362	0.370	0.535	0.599	0.564	0.516	0.353	0.280	0.242	0.311

SU YILI (2006) YILLIK TOPLAM AKIM 4.86 MİLYON M3 43 MM. 1.4 LT/SN/Km2

12. Sakarya Havzasi

D12A054 PORSUK Ç. EŞENKARA

YERİ : **ESKİŞEHİR PORSUK BARAJI YOLUNUN 18KM DEDİR**
30°25'28" Doğu - 39°43'54" Kuzey

YAĞIŞ ALANI : **5169.00 km2** **YAKLAŞIK KOT : 807 m**

GÖZLEM SÜRESİ : **01.07.1963 - 30.09.2006**

ORTALAMA AKIMLAR : **Gözlem süresinde 10.899 m3/sn. (41 Yıllık) 2006 Su yılında 6.876 m3/sn.**

ANLIK EN ÇOK VE EN AZ AKIMLAR:

2006 Su yılında anlık ençok akım	**:**	**18.0**	**m3/sn**	**27.02.2006**
2006 Su yılında anlık enaz akım	**:**	**1.21**	**m3/sn**	**10.09.2006**
Gözlem süresinde anlık ençok akım	**:**	**240.**	**m3/sn**	**09.03.1964**
Gözlem süresinde anlık enaz akım	**:**	**0.001**	**m3/sn**	**05.08.2004**

1. Anahtar Eğrisi (Seviyeler cm olarak)

Seviye	Akım	Seviye	Akım	Seviye	Akım
1	0.000	111	11.6	145	23.4
51	0.886	113	12.6	163	31.6
61	1.4	123	15.4	181	42.8
71	2.5	131	18.0	198	53.5
101	8.8	141	22.0		

Akımlar 01 Ekim 2005 'den 30 Eylül 2006' a kadar m3/sn olarak

Gün	Ekim	Kasım	Aralık	Ocak	Şubat	Mart	Nisan	Mayıs	Haziran	Temmuz	Ağustos	Eylül
01	3.13	2.50	2.07	2.18	7.33	9.64	3.13	13.4	13.4	11.6	12.6	8.17
02	2.92	2.39	2.07	2.18	7.33	9.08	2.92	13.4	13.7	12.1	12.6	7.96
03	2.71	2.28	2.07	2.18	7.33	8.80	2.92	13.4	13.7	11.6	12.6	7.75
04	2.50	2.28	2.07	2.18	7.33	9.64	2.50	13.4	13.7	11.3	12.6	7.54
05	2.39	2.28	2.07	2.18	7.33	8.38	2.39	13.7	13.7	11.3	12.6	6.49
06	2.18	2.28	2.07	2.28	7.33	6.70	2.39	13.7	13.7	11.6	12.6	2.50
07	2.18	2.28	2.07	2.18	7.33	5.86	2.39	13.4	13.7	11.6	12.6	1.74
08	2.18	2.28	2.07	2.18	7.33	5.65	2.28	12.9	13.7	12.1	12.9	1.42
09	2.18	2.07	2.07	2.18	7.33	5.44	2.39	12.9	13.7	12.1	12.9	1.26
10	2.18	1.96	2.07	2.18	7.33	5.02	2.39	12.9	13.7	12.1	13.2	1.21
11	2.18	1.96	2.07	2.18	7.75	5.23	2.28	12.6	13.4	12.6	13.2	1.31
12	2.50	1.96	2.07	2.18	9.36	5.65	2.28	12.6	13.2	12.6	13.2	1.42
13	3.13	1.96	2.07	2.18	8.80	5.86	2.28	12.6	12.9	12.6	13.2	1.85
14	3.34	1.96	2.07	2.18	8.38	5.65	2.28	12.6	12.6	12.6	13.2	2.07
15	3.34	1.96	2.07	2.18	8.17	5.23	2.28	12.6	12.1	12.6	13.2	2.28
16	3.34	1.96	2.07	2.18	8.17	4.81	3.13	11.6	11.3	12.6	13.2	2.18
17	3.34	1.96	2.07	2.18	8.17	4.60	4.60	11.6	11.3	12.6	12.9	1.96
18	3.34	1.96	2.07	2.18	7.96	4.18	5.65	11.3	11.3	12.6	12.6	1.96
19	3.34	1.96	2.07	2.18	7.75	4.39	6.49	11.3	11.3	12.6	12.6	1.96
20	3.34	2.07	2.07	2.18	8.38	4.18	8.17	10.8	11.3	12.6	12.6	1.96
21	3.34	2.07	2.07	2.18	9.92	3.97	9.64	10.8	11.6	12.6	12.6	1.96
22	3.34	1.96	2.07	2.18	10.8	3.76	9.92	10.5	12.6	12.6	12.6	1.96
23	3.34	1.96	2.07	2.28	8.59	3.76	9.92	10.8	12.6	12.6	12.6	1.96
24	3.34	2.07	2.07	2.28	7.75	3.97	10.8	11.3	12.6	12.6	12.6	1.96
25	3.34	2.07	2.07	2.28	8.59	4.18	11.0	12.9	12.6	12.6	12.6	1.96
26	3.34	2.07	2.07	2.28	14.0	3.76	11.6	13.2	12.6	12.6	12.6	1.96
27	3.34	2.18	2.07	2.28	13.7	3.34	12.9	13.4	12.6	12.6	12.6	1.96
28	3.34	2.07	2.07	2.28	10.5	3.13	13.2	13.2	12.6	12.6	12.1	1.96
29	3.34	2.07	2.18	4.39	-----	3.13	13.2	13.4	12.6	12.6	11.6	1.96
30	2.92	2.07	2.18	5.02	-----	3.13	13.4	13.4	11.3	12.6	11.6	1.96
31	2.71	-----	2.18	7.33	-----	3.13	-----	13.4	-----	12.6	11.3	-----
Maks.	3.34	12.6	3.55	7.33	18.0	11.0	13.7	14.0	14.3	12.6	13.2	8.17
Min.	2.18	1.42	1.74	2.07	1.53	3.13	2.28	10.5	11.3	11.3	11.3	1.21
Ortalama	2.95	2.10	2.08	2.53	8.57	5.27	6.02	12.5	12.7	12.3	12.6	2.82
LT/SN/Km2	0.571	0.406	0.403	0.490	1.66	1.02	1.17	2.43	2.46	2.38	2.45	0.545
AKIM mm.	1.53	1.05	1.08	1.31	4.01	2.73	3.02	6.50	6.37	6.39	6.55	1.41
MİL. M3	7.90	5.43	5.57	6.78	20.7	14.1	15.6	33.6	32.9	33.0	33.9	7.31

SU YILI (2006) YILLIK TOPLAM AKIM 216.79 MİLYON M3 42 MM. 1.3 LT/SN/Km2

12. Sakarya Havzasi

D12A055 MURAT Ç. AKÇAKÖY

YERİ : ALTINTAŞ A 7 KM MESAFEDEKİ AKÇAKOYUN 1.5 KM MENBAINDADIR.
30°2'0" Doğu - 30°3'0" Kuzey

YAĞIŞ ALANI : 297.00 km2 **YAKLAŞIK KOT :** 1062 m

GÖZLEM SÜRESİ : 01.05.1964 - 30.09.2006

ORTALAMA AKIMLAR : Gözlem süresinde 1.179 m3/sn. (40 Yıllık) 2006 Su yılında 1.232 m3/sn.

ANLIK EN ÇOK VE EN AZ AKIMLAR:

2006 Su yılında anlık ençok akım	:	11.8	m3/sn	12.02.2006
2006 Su yılında anlık enaz akım	:	0.000	m3/sn	01.10.2005
Gözlem süresinde anlık ençok akım	:	50.0	m3/sn	12.03.1968
Gözlem süresinde anlık enaz akım	:	0.000	m3/sn	17.08.1973

13. Anahtar Eğrisi (Seviyeler cm olarak)

Seviye	Akım	Seviye	Akım	Seviye	Akım	Seviye	Akım
1	0.003	16	0.630	90	5.2	220	17.8
4	0.052	19	0.790	120	7.0	230	19.1
7	0.160	30	1.4	150	9.5	240	20.4
10	0.300	45	2.4	180	12.6	250	21.7
13	0.450	60	3.4	210	16.5		

Akımlar 01 Ekim 2005 'den 30 Eylül 2006' a kadar m3/sn olarak

Gün	Ekim	Kasım	Aralık	Ocak	Şubat	Mart	Nisan	Mayıs	Haziran	Temmuz	Ağustos	Eylül
01	KURU	0.029	0.160	0.500	2.32	6.13	3.36	1.88	0.884	0.300	0.052	KURU
02	KURU	0.029	0.160	0.560	2.00	5.95	3.23	1.88	0.830	0.300	0.052	KURU
03	KURU	0.029	0.160	0.500	1.58	7.92	3.17	1.82	0.740	0.250	0.029	KURU
04	KURU	0.029	0.160	0.450	1.34	8.59	3.10	1.76	0.740	0.250	0.029	KURU
05	KURU	0.029	0.160	0.630	1.34	6.73	3.04	1.94	0.740	0.250	0.029	KURU
06	KURU	0.029	0.120	1.28	1.28	5.95	2.86	1.88	0.680	0.200	0.012	KURU
07	KURU	0.029	0.120	1.05	1.16	5.53	2.80	1.94	0.630	0.250	0.012	KURU
08	KURU	0.029	0.120	0.884	1.10	6.07	2.80	2.00	0.680	0.200	0.003	KURU
09	KURU	0.029	0.120	0.740	0.884	6.07	2.80	1.94	0.630	0.200	0.003	KURU
10	KURU	0.029	0.120	0.680	0.992	5.29	2.80	1.82	0.630	0.200	0.003	KURU
11	KURU	0.029	0.160	0.630	6.25	4.87	2.80	1.70	0.680	0.200	0.003	KURU
12	KURU	0.029	0.160	0.560	9.58	4.63	2.72	1.70	0.790	0.200	0.003	KURU
13	KURU	0.029	0.160	0.500	5.35	4.63	2.72	1.76	0.740	0.200	0.003	KURU
14	KURU	0.029	0.160	0.500	3.85	5.65	2.80	1.70	0.680	0.200	0.003	KURU
15	KURU	0.029	0.160	0.450	3.17	6.25	3.23	1.58	0.740	0.200	0.003	KURU
16	KURU	0.029	0.160	0.450	2.40	5.35	3.10	1.64	0.680	0.160	0.003	KURU
17	KURU	0.029	0.160	0.450	2.16	4.93	2.86	1.58	0.630	0.160	0.003	KURU
18	0.003	0.029	0.160	0.450	2.32	4.51	2.72	1.52	0.630	0.160	KURU	KURU
19	0.012	0.029	0.938	0.450	3.67	4.27	2.56	1.40	0.560	0.160	KURU	KURU
20	0.012	0.052	1.10	3.79	4.03	3.85	2.56	1.40	0.500	0.160	KURU	KURU
21	0.012	0.082	0.830	1.34	4.63	3.61	2.56	1.34	0.450	0.120	KURU	KURU
22	0.012	0.082	1.70	0.938	4.33	3.49	2.56	1.22	0.400	0.120	KURU	KURU
23	0.012	0.082	1.94	0.790	4.21	3.49	2.64	1.22	0.400	0.120	KURU	KURU
24	0.012	0.082	1.22	0.790	4.03	3.97	2.80	1.16	0.350	0.120	KURU	KURU
25	0.012	0.082	0.400	0.790	5.47	4.57	2.56	1.16	0.350	0.082	KURU	KURU
26	0.012	0.160	0.400	0.680	6.61	4.39	2.32	1.16	0.350	0.082	KURU	KURU
27	0.012	0.200	0.350	0.560	7.27	4.03	2.24	1.10	0.350	0.082	KURU	KURU
28	0.012	0.160	0.350	0.830	6.37	3.73	2.08	1.05	0.350	0.082	KURU	KURU
29	0.012	0.160	0.350	1.70	-----	3.49	2.08	0.938	0.350	0.082	KURU	KURU
30	0.012	0.160	0.400	2.16	-----	3.43	2.00	0.938	0.350	0.082	KURU	KURU
31	0.012	-----	0.450	2.00	-----	3.43	-----	0.884	-----	0.082	KURU	-----
Maks.	0.012	0.200	2.64	5.65	11.8	10.8	3.43	2.16	0.938	0.350	0.052	KURU
Min.	KURU	0.029	0.120	0.450	0.884	3.43	2.00	0.884	0.350	0.082	KURU	KURU
Ortalama	0.005	0.062	0.423	0.906	3.56	4.99	2.73	1.52	0.584	0.169	0.008	KURU
LT/SN/Km2	0.017	0.208	1.42	3.05	12.0	16.8	9.19	5.11	1.97	0.571	0.027	0.000
AKIM mm.	0.046	0.539	3.81	8.17	29.0	45.0	23.8	13.7	5.09	1.53	0.071	0.000
MİL. M3	0.014	0.160	1.13	2.43	8.61	13.4	7.07	4.06	1.51	0.454	0.021	0.000

SU YILI (2006) YILLIK TOPLAM AKIM 38.86 MİLYON M3 131 MM. 4.1 LT/SN/Km2

12. Sakarya Havzasi

D12A063 ULU DERE ULUÇAYIR

YERİ : **ESKİŞEHİR PORSUK BARAJ YOLUNUN 20 KM SİNDEKİ GÖKÇEK IŞIK KÖYÜNDEN SOLA AYRILAN YÖRÜK KIRKAKÖY YOLUNUN 3 KM SİNDEKİ ULUÇAYIR KÖYÜNDEDİR. 25 LİK PAFTADAKİ YERİ: İ24 30°24'0" Doğu - 39°38'0" Kuzey**

YAĞIŞ ALANI : **290.70 km2** **YAKLAŞIK KOT : 826 m**

GÖZLEM SÜRESİ : **01.05.1964 - 30.09.2006**

ORTALAMA AKIMLAR : **Gözlem süresinde 0.707 m3/sn. (42 Yıllık) 2006 Su yılında 0.625 m3/sn.**

ANLIK EN ÇOK VE EN AZ AKIMLAR:

2006 Su yılında anlık ençok akım	**:**	**28.4**	**m3/sn**	**26.02.2006**
2006 Su yılında anlık enaz akım	**:**	**0.005**	**m3/sn**	**08.11.2005**
Gözlem süresinde anlık ençok akım	**:**	**54.4**	**m3/sn**	**18.12.2001**
Gözlem süresinde anlık enaz akım	**:**	**0.000**	**m3/sn**	**01.09.1998**

12. Anahtar Eğrisi (Seviyeler cm olarak)

Seviye	Akım	Seviye	Akım	Seviye	Akım	Seviye	Akım
10	0.003	20	0.047	30	0.834	70	11.3
13	0.006	22	0.132	35	1.4	80	15.0
14	0.008	24	0.215	40	2.3	90	18.5
16	0.012	26	0.400	50	4.7	114	29.8
18	0.021	28	0.590	60	7.7	130	38.7

Akımlar 01 Ekim 2005 'den 30 Eylül 2006' a kadar m3/sn olarak

Gün	Ekim	Kasım	Aralık	Ocak	Şubat	Mart	Nisan	Mayıs	Haziran	Temmuz	Ağustos	Eylül
01	0.215	0.400	0.308	0.308	0.400	5.04	1.06	0.495	0.132	0.308	0.034	0.132
02	0.215	0.400	0.308	0.308	0.400	4.74	0.949	0.495	0.174	0.308	0.034	0.132
03	0.215	0.400	0.308	0.308	0.400	5.33	0.949	0.495	0.090	0.308	0.034	0.174
04	0.215	0.400	0.308	0.308	0.400	5.04	0.712	0.495	0.090	0.215	0.034	0.132
05	0.215	0.400	0.308	0.308	0.400	4.74	0.712	0.495	0.090	0.174	0.021	0.132
06	0.215	0.400	0.308	0.495	0.400	3.76	0.712	0.590	0.047	0.132	0.017	0.090
07	0.215	0.400	0.308	0.495	0.495	3.03	0.949	0.590	0.047	0.132	0.017	0.132
08	0.215	0.308	0.308	0.495	0.495	2.79	0.949	0.712	0.047	0.090	0.021	0.132
09	0.215	0.308	0.308	0.495	0.495	2.79	0.949	0.712	0.047	0.090	0.021	0.132
10	0.215	0.308	0.308	0.400	0.495	2.30	0.949	0.834	0.090	0.090	0.017	0.132
11	0.215	0.308	0.308	0.400	1.06	2.54	0.949	0.590	0.090	0.090	0.021	0.174
12	0.215	0.308	0.308	0.400	2.54	3.28	0.834	0.590	0.174	0.047	0.021	0.132
13	0.215	0.308	0.308	0.400	1.77	3.76	0.712	0.495	0.215	0.090	0.017	0.174
14	0.215	0.308	0.308	0.400	1.18	3.52	0.712	0.495	0.308	0.090	0.012	0.174
15	0.215	0.308	0.308	0.400	1.06	3.28	0.712	0.495	0.215	0.090	0.017	0.174
16	0.215	0.308	0.308	0.400	0.949	2.30	0.712	0.590	0.215	0.034	0.017	0.174
17	0.215	0.308	0.308	0.400	0.834	1.77	0.590	0.712	0.215	0.047	0.021	0.174
18	0.215	0.308	0.308	0.400	0.834	1.59	0.495	0.590	0.215	0.047	0.034	0.215
19	0.215	0.308	0.308	0.400	1.06	1.59	0.400	0.590	0.215	0.047	0.034	0.215
20	0.308	0.308	0.308	0.400	1.94	1.59	0.400	0.590	0.215	0.034	0.034	0.215
21	0.308	0.215	0.308	0.400	3.52	1.41	0.400	0.495	0.215	0.047	0.021	0.308
22	0.308	0.215	0.308	0.400	4.01	1.29	0.400	0.400	0.215	0.034	0.017	0.400
23	0.215	0.215	0.308	0.495	4.01	1.29	0.308	0.400	0.174	0.034	0.017	0.400
24	0.215	0.215	0.308	0.495	3.52	1.59	0.308	0.308	0.174	0.047	0.034	0.400
25	0.215	0.215	0.308	0.495	7.40	1.59	0.308	0.308	0.132	0.034	0.047	0.400
26	0.215	0.308	0.308	0.495	9.13	1.41	0.308	0.308	0.090	0.034	0.047	0.400
27	0.215	0.308	0.308	0.495	6.51	1.29	0.308	0.308	0.132	0.017	0.047	0.400
28	0.215	0.308	0.308	0.495	5.04	1.18	0.308	0.215	0.215	0.021	0.047	0.400
29	0.215	0.308	0.308	0.400	-----	1.06	0.308	0.215	0.400	0.034	0.047	0.400
30	0.215	0.308	0.308	0.400	-----	1.06	0.400	0.174	0.308	0.034	0.047	0.495
31	0.215	-----	0.308	0.400	-----	1.06	-----	0.132	-----	0.034	0.047	-----
Maks.	0.400	0.834	0.308	0.495	28.4	6.81	1.06	3.28	0.495	0.308	0.090	0.495
Min.	0.215	0.005	0.308	0.308	0.400	1.06	0.308	0.005	0.021	0.006	0.008	0.047
Ortalama	0.224	0.314	0.308	0.416	2.17	2.55	0.625	0.481	0.166	0.091	0.029	0.238
LT/SN/Km2	0.771	1.08	1.06	1.43	7.46	8.77	2.15	1.65	0.572	0.314	0.099	0.819
AKIM mm.	2.06	2.80	2.84	3.83	18.1	23.5	5.58	4.43	1.48	0.842	0.266	2.12
MİL. M3	0.600	0.814	0.825	1.11	5.25	6.83	1.62	1.29	0.431	0.245	0.077	0.617

SU YILI (2006) YILLIK TOPLAM AKIM 19.71 MİLYON M3 68 MM. 2.1 LT/SN/Km2

12. Sakarya Havzasi

D12A075 SİRKELİ ÇAYI KARŞIYAKA

YERİ : **ANKARA-ÇUBUK YOLUNUN 24.KM SİNDEN SOLA AYRILAN SİRKELİ BUCAĞI YOLUNUN 8,5 KM. SİNDEKİ KARŞIYAKA KÖYÜNÜN 200 M. İLERİSİNDEKİ KÖPRÜNÜN 60 M. MANSABINDADIR. 32°53'20" Doğu - 40°8'30" Kuzey**

YAĞIŞ ALANI : **59.20 km2** **YAKLAŞIK KOT : 1002 m**

GÖZLEM SÜRESİ : **10.07.1964 - 30.09.2006**

ORTALAMA AKIMLAR : **Gözlem süresinde 0.249 m3/sn. (40 Yıllık) 2006 Su yılında 0.073 m3/sn.**

ANLIK EN ÇOK VE EN AZ AKIMLAR:

2006 Su yılında anlık ençok akım	**:**	**3.00**	**m3/sn**	**02.03.2006**
2006 Su yılında anlık enaz akım	**:**	**0.000**	**m3/sn**	**01.10.2005**
Gözlem süresinde anlık ençok akım	**:**	**92.0**	**m3/sn**	**11.08.1971**
Gözlem süresinde anlık enaz akım	**:**	**0.000**	**m3/sn**	**08.01.1965**

13. Anahtar Eğrisi (Seviyeler cm olarak)

Seviye	Akım	Seviye	Akım	Seviye	Akım	Seviye	Akım
1	0.008	11	0.450	21	1.8	35	6.0
3	0.046	13	0.640	23	2.2	50	11.2
5	0.115	15	0.860	25	2.7	70	19.7
7	0.200	17	1.1	27	3.3	90	28.9
9	0.305	19	1.4	29	3.9	100	33.8

Akımlar 01 Ekim 2005 'den 30 Eylül 2006' a kadar m3/sn olarak

Gün	Ekim	Kasım	Aralık	Ocak	Şubat	Mart	Nisan	Mayıs	Haziran	Temmuz	Ağustos	Eylül
01	KURU	0.023	0.046	0.046	0.080	0.370	0.200	0.080	0.008	KURU	KURU	KURU
02	KURU	0.023	0.046	0.080	0.080	1.10	0.200	0.080	0.008	KURU	KURU	KURU
03	0.008	0.023	0.046	0.080	0.080	0.740	0.200	0.080	0.008	0.008	KURU	KURU
04	0.008	0.023	0.046	0.080	0.080	0.540	0.200	0.080	0.008	0.008	KURU	KURU
05	0.008	0.023	0.046	0.080	0.080	0.540	0.200	0.080	0.008	KURU	KURU	KURU
06	0.008	0.023	0.046	0.080	0.080	0.370	0.200	0.080	0.008	KURU	KURU	KURU
07	0.008	0.023	0.046	0.080	0.080	0.370	0.200	0.080	0.008	KURU	KURU	KURU
08	0.008	0.046	0.046	0.080	0.080	0.370	0.200	0.080	0.008	KURU	KURU	KURU
09	0.008	0.046	0.046	0.080	0.080	0.305	0.155	0.115	0.008	KURU	KURU	KURU
10	0.008	0.046	0.046	0.080	0.080	0.305	0.155	0.115	0.008	KURU	KURU	KURU
11	0.008	0.046	0.046	0.080	0.080	0.305	0.155	0.115	0.008	KURU	KURU	KURU
12	0.023	0.046	0.046	0.080	0.080	0.305	0.155	0.115	0.008	KURU	KURU	KURU
13	0.023	0.046	0.046	0.080	0.080	0.305	0.155	0.115	0.008	KURU	KURU	KURU
14	0.023	0.046	0.046	0.080	0.080	0.305	0.200	0.080	0.008	KURU	KURU	KURU
15	0.023	0.046	0.046	0.080	0.080	0.250	0.155	0.080	0.008	KURU	KURU	KURU
16	0.023	0.046	0.046	0.080	0.080	0.370	0.155	0.080	0.008	KURU	KURU	KURU
17	0.023	0.046	0.046	0.080	0.080	0.370	0.155	0.080	0.008	KURU	KURU	KURU
18	0.023	0.046	0.046	0.080	0.080	0.370	0.115	0.080	0.008	KURU	KURU	KURU
19	0.023	0.046	0.046	0.080	0.080	0.370	0.115	0.080	0.008	KURU	KURU	KURU
20	0.023	0.046	0.046	0.080	0.080	0.370	0.115	0.080	0.008	KURU	KURU	KURU
21	0.023	0.046	0.046	0.080	0.080	0.370	0.115	0.080	0.008	KURU	KURU	KURU
22	0.023	0.046	0.046	0.080	0.080	0.305	0.115	0.046	0.008	KURU	KURU	KURU
23	0.023	0.046	0.046	0.080	0.080	0.305	0.115	0.046	0.008	KURU	KURU	KURU
24	0.023	0.046	0.046	0.080	0.080	0.305	0.115	0.046	KURU	KURU	KURU	KURU
25	0.023	0.046	0.046	0.080	0.115	0.305	0.115	0.023	KURU	KURU	KURU	KURU
26	0.023	0.046	0.046	0.080	0.155	0.250	0.115	0.023	KURU	KURU	KURU	KURU
27	0.023	0.046	0.046	0.080	0.200	0.250	0.115	0.023	KURU	KURU	KURU	KURU
28	0.023	0.046	0.046	0.080	0.250	0.250	0.115	0.008	KURU	KURU	KURU	KURU
29	0.023	0.046	0.046	0.080	-----	0.250	0.115	0.008	0.008	KURU	KURU	KURU
30	0.023	0.046	0.046	0.080	-----	0.250	0.115	0.008	KURU	KURU	KURU	KURU
31	0.023	-----	0.046	0.080	-----	0.200	-----	0.008	-----	KURU	KURU	-----
Maks.	0.023	0.046	0.046	0.115	0.305	3.00	0.250	0.155	0.023	0.008	KURU	KURU
Min.	KURU	0.023	0.046	0.046	0.080	0.200	0.115	0.008	KURU	KURU	KURU	KURU
Ortalama	0.017	0.041	0.046	0.079	0.094	0.367	0.151	0.068	0.006	0.001	KURU	KURU
LT/SN/Km2	0.290	0.686	0.777	1.33	1.59	6.20	2.55	1.14	0.108	0.009	0.000	0.000
AKIM mm.	0.776	1.78	2.08	3.57	3.85	16.6	6.62	3.06	0.280	0.023	0.000	0.000
MİL. M3	0.046	0.105	0.123	0.211	0.228	0.982	0.392	0.181	0.017	0.001	0.000	0.000

SU YILI (2006) YILLIK TOPLAM AKIM 2.29 MİLYON M3 39 MM. 1.2 LT/SN/Km2

12. Sakarya Havzasi

D12A083 RAVLI DERESİ RAVLI

YERİ : **ANKARA-ÇANKIRI YOLUNUN 50. KM SİNDEKİ AKYURT(RAVLI) İLÇESİNİN 2 KM. MENBASINDA ÇİFTLİĞİN İÇİNDEDİR.**
33°6'30" Doğu - 40°8'4" Kuzey

YAĞIŞ ALANI : **65.30 km2** **YAKLAŞIK KOT : 1051 m**

GÖZLEM SÜRESİ : **12.12.1965 - 30.09.2006**

ORTALAMA AKIMLAR : **Gözlem süresinde 0.160 m3/sn. (21 Yıllık) 2006 Su yılında 0.086 m3/sn.**

ANLIK EN ÇOK VE EN AZ AKIMLAR:

2006 Su yılında anlık ençok akım	:	**5.04**	**m3/sn**	**03.03.2006**
2006 Su yılında anlık enaz akım	:	**0.005**	**m3/sn**	**14.02.2006**
Gözlem süresinde anlık ençok akım	:	**7.80**	**m3/sn**	**01.05.1980**
Gözlem süresinde anlık enaz akım	:	**0.000**	**m3/sn**	**18.02.2005**

İstasyon için kullanılmış anahtar bulunamadı.

Akımlar 01 Ekim 2005 'den 30 Eylül 2006' a kadar m3/sn olarak

Gün	Ekim	Kasım	Aralık	Ocak	Şubat	Mart	Nisan	Mayıs	Haziran	Temmuz	Ağustos	Eylül
01	0.045	0.045	0.015	0.015	0.015	0.015	0.392	0.328	0.328	0.030	0.110	0.045
02	0.045	0.045	0.015	0.015	0.015	0.015	0.392	0.328	0.045	0.030	0.070	0.045
03	0.045	0.045	0.015	0.015	0.015	0.392	0.392	0.328	0.045	0.030	0.045	0.045
04	0.045	0.045	0.015	0.015	0.015	0.200	0.392	0.264	0.045	0.030	0.045	0.045
05	0.045	0.045	0.015	0.015	0.015	0.110	0.392	0.264	0.045	0.045	0.045	0.030
06	0.045	0.045	0.015	0.015	0.015	0.110	0.328	0.264	0.045	0.030	0.045	0.030
07	0.045	0.045	0.015	0.015	0.030	0.110	0.328	0.264	0.045	0.030	0.045	0.045
08	0.045	0.045	0.015	0.015	0.015	0.155	0.264	0.264	0.045	0.030	0.045	0.045
09	0.045	0.045	0.015	0.015	0.015	0.200	0.264	0.200	0.045	0.030	0.030	0.045
10	0.045	0.045	0.015	0.015	0.015	0.070	0.264	0.200	0.045	0.030	0.030	0.045
11	0.045	0.045	0.015	0.015	0.015	0.110	0.264	0.200	0.045	0.045	0.030	0.045
12	0.045	0.045	0.015	0.015	0.015	0.070	0.200	0.200	0.045	0.045	0.030	0.045
13	0.045	0.045	0.015	0.015	0.015	0.155	0.264	0.200	0.045	0.045	0.030	0.045
14	0.045	0.030	0.015	0.015	0.015	0.264	0.264	0.110	0.045	0.030	0.045	0.045
15	0.045	0.030	0.015	0.015	0.015	0.264	0.264	0.110	0.045	0.045	0.045	0.045
16	0.045	0.030	0.015	0.015	0.015	0.200	0.328	0.110	0.030	0.155	0.045	0.045
17	0.045	0.030	0.015	0.015	0.015	0.200	0.328	0.110	0.030	0.070	0.030	0.045
18	0.045	0.030	0.015	0.015	0.015	0.200	0.328	0.110	0.030	0.045	0.045	0.045
19	0.045	0.030	0.015	0.015	0.015	0.264	0.328	0.110	0.030	0.045	0.045	0.045
20	0.045	0.030	0.015	0.015	0.015	0.264	0.328	0.110	0.045	0.030	0.030	0.045
21	0.045	0.030	0.015	0.015	0.015	0.264	0.264	0.110	0.045	0.030	0.030	0.045
22	0.045	0.030	0.015	0.015	0.015	0.264	0.264	0.110	0.045	0.030	0.030	0.045
23	0.045	0.030	0.015	0.015	0.015	0.328	0.264	0.110	0.045	0.045	0.030	0.045
24	0.045	0.030	0.015	0.015	0.015	0.456	0.264	0.110	0.045	0.045	0.045	0.045
25	0.045	0.030	0.015	0.015	0.015	0.520	0.264	0.110	0.045	0.045	0.045	0.045
26	0.045	0.030	0.015	0.015	0.015	0.456	0.264	0.110	0.045	0.030	0.045	0.045
27	0.030	0.030	0.015	0.015	0.030	0.392	0.264	0.110	0.045	0.030	0.030	0.045
28	0.030	0.030	0.015	0.015	0.015	0.392	0.264	0.110	0.045	0.045	0.030	0.045
29	0.045	0.030	0.015	0.015	-----	0.392	0.264	0.110	0.045	0.045	0.045	0.045
30	0.045	0.030	0.015	0.015	-----	0.392	0.328	0.110	0.045	0.045	0.045	0.045
31	0.045	-----	0.015	0.015	-----	0.392	-----	0.110	-----	0.045	0.045	-----
Maks.	0.110	0.045	0.030	0.030	0.030	5.04	0.456	3.55	0.328	0.155	0.200	0.045
Min.	0.030	0.015	0.015	0.015	0.005	0.015	0.110	0.005	0.030	0.030	0.030	0.030
Ortalama	0.044	0.037	0.015	0.015	0.016	0.246	0.300	0.170	0.052	0.042	0.042	0.044
LT/SN/Km2	0.674	0.559	0.230	0.230	0.246	3.76	4.60	2.61	0.803	0.645	0.645	0.674
AKIM mm.	1.81	1.45	0.615	0.615	0.595	10.1	11.9	6.99	2.08	1.73	1.73	1.75
MİL. M3	0.118	0.095	0.040	0.040	0.039	0.658	0.778	0.457	0.136	0.113	0.113	0.114

SU YILI (2006) YILLIK TOPLAM AKIM 2.70 MİLYON M3 41 MM. 1.3 LT/SN/Km2

12. Sakarya Havzasi

D12A091 GÖYNÜK S. KAŞIKÇI

YERİ : OSMANELİ-SAKARYA KÖPRÜSÜNDEN GEÇİLEREK SAKARYA NEHRİNİNMENBAĞINA DOĞRU 15.KM.DE KAŞIKCI KÖPRÜSÜNDEDİR.LİMNIGRAFLI.
30°9'0" Doğu - 40°20'0" Kuzey

YAĞIŞ ALANI : 968.00 km2 **YAKLAŞIK KOT** : 129 m

GÖZLEM SÜRESİ : 01.10.1983 - 30.09.2006

ORTALAMA AKIMLAR : Gözlem süresinde 5.246 m3/sn. (11 Yıllık) 2006 Su yılında 4.155 m3/sn.

ANLIK EN ÇOK VE EN AZ AKIMLAR:

2006 Su yılında anlık ençok akım	:	26.3	m3/sn	03.03.2006
2006 Su yılında anlık enaz akım	:	0.074	m3/sn	22.08.2006
Gözlem süresinde anlık ençok akım	:	48.0	m3/sn	13.01.1982
Gözlem süresinde anlık enaz akım	:	0.010	m3/sn	05.09.1992

4. Anahtar Eğrisi (Seviyeler cm olarak)

Seviye	Akım	Seviye	Akım	Seviye	Akım	Seviye	Akım
20	0.029	55	2.1	130	12.5	306	35.0
24	0.053	65	3.4	162	16.6	320	36.4
28	0.102	75	4.8	193	20.7	334	37.9
35	0.357	85	6.4	225	24.8	365	40.3
45	1.1	100	8.2	268	30.4	398	45.5

Akımlar 01 Ekim 2005 'den 30 Eylül 2006' a kadar m3/sn olarak

Gün	Ekim	Kasım	Aralık	Ocak	Şubat	Mart	Nisan	Mayıs	Haziran	Temmuz	Ağustos	Eylül
01	0.944	1.20	3.68	6.08	3.68	16.8	12.2	5.60	0.944	0.235	0.194	0.194
02	0.944	1.20	3.28	5.44	3.68	16.3	11.9	5.60	0.944	0.194	0.194	0.498
03	0.944	1.40	3.16	5.12	3.68	19.4	11.6	5.60	0.865	0.235	0.194	0.709
04	0.944	1.40	3.04	4.96	3.82	19.7	11.4	5.44	0.865	0.498	0.153	0.944
05	0.944	1.70	2.80	4.80	3.82	18.5	10.9	5.44	0.865	0.568	0.153	0.944
06	0.944	1.90	2.80	5.12	4.10	17.5	10.6	5.44	0.865	0.568	0.153	1.02
07	0.944	2.10	2.66	5.28	4.52	16.9	10.3	5.44	0.865	0.568	0.153	1.10
08	0.944	2.66	2.66	5.28	4.38	18.7	10.1	5.44	0.865	0.427	0.153	1.10
09	0.944	1.90	2.66	4.96	4.24	17.7	9.77	5.44	0.865	0.427	0.153	1.10
10	0.944	1.80	2.52	4.96	4.52	16.8	9.63	5.44	0.865	0.316	0.153	1.10
11	0.944	1.90	2.52	4.80	12.6	16.9	9.34	5.28	0.865	0.235	0.153	1.10
12	0.944	1.70	2.38	4.66	10.6	17.2	9.06	5.28	0.865	0.235	0.153	1.10
13	0.865	1.10	2.38	4.38	8.77	17.5	8.77	5.28	0.865	0.194	0.153	1.10
14	0.865	1.10	2.24	4.24	7.90	17.8	8.49	4.96	0.865	0.316	0.153	1.10
15	0.865	1.10	2.24	4.10	7.15	18.1	8.20	4.96	0.865	0.357	0.153	1.10
16	0.865	1.10	2.24	4.10	6.70	16.9	7.90	4.38	0.865	0.316	0.153	1.10
17	0.944	0.944	2.80	3.96	6.58	17.7	7.60	4.10	0.865	0.316	0.153	1.10
18	0.944	1.50	2.66	4.10	6.52	16.3	7.30	4.52	0.865	0.275	0.153	1.10
19	0.865	1.90	2.80	4.24	7.30	16.0	7.00	4.52	0.865	0.275	0.153	1.10
20	0.787	2.24	2.80	5.44	11.5	15.2	6.70	4.38	0.787	0.275	0.153	1.30
21	0.787	2.38	2.66	4.38	14.0	14.5	6.58	3.96	0.787	0.235	0.153	1.70
22	0.787	2.00	2.52	4.24	13.4	14.1	6.52	4.24	0.709	0.235	0.153	2.10
23	0.787	2.00	2.52	4.24	13.9	14.1	6.46	3.96	0.498	0.235	0.194	2.00
24	0.787	1.90	2.52	4.10	14.1	14.5	6.40	3.68	0.357	0.194	0.194	1.80
25	0.787	2.92	2.38	4.24	14.1	14.9	6.24	2.38	0.357	0.194	0.194	1.40
26	0.787	4.96	2.38	4.10	15.8	14.5	5.92	2.38	0.357	0.194	0.194	1.20
27	0.787	4.24	2.38	3.82	17.5	13.9	5.76	1.90	0.275	0.194	0.194	1.10
28	0.865	4.10	2.80	3.68	17.2	13.4	5.60	1.60	0.235	0.194	0.194	0.709
29	1.02	3.96	4.52	3.68	-----	13.0	5.76	1.70	0.275	0.194	0.194	0.568
30	1.02	4.38	4.66	3.54	-----	12.8	5.60	1.02	0.275	0.194	0.194	0.498
31	1.10	-----	5.76	3.54	-----	12.5	-----	0.944	-----	0.194	0.194	-----
Maks.	1.10	6.85	8.20	8.20	19.0	26.3	12.6	5.60	0.944	0.639	0.568	2.10
Min.	0.787	0.944	2.24	3.54	3.68	12.2	5.60	0.235	0.194	0.194	0.074	0.088
Ortalama	0.898	2.16	2.88	4.50	8.79	16.1	8.32	4.20	0.717	0.293	0.169	1.10
LT/SN/Km2	0.928	2.23	2.98	4.65	9.08	16.7	8.60	4.34	0.741	0.303	0.174	1.14
AKIM mm.	2.49	5.77	7.98	12.5	22.0	44.6	22.3	11.6	1.92	0.811	0.467	2.94
MİL. M3	2.41	5.59	7.73	12.1	21.3	43.2	21.6	11.3	1.86	0.785	0.452	2.85

SU YILI (2006) YILLIK TOPLAM AKIM 131.18 MİLYON M3 136 MM. 4.3 LT/SN/Km2

12. Sakarya Havzasi

D12A093 KOKAR Ç. EYİCE

YERİ : **ALTINTAŞA 20 KM.UZAKLIKTAKİ CALKÖY-SİNCANLI YOLLARININ5.KMSİNDEKİ EYİCE KÖYÜNDEDİR**

30°10'0" Doğu - 36°53'0" Kuzey

YAĞIŞ ALANI : **153.10 km2** **YAKLAŞIK KOT : 1130 m**

GÖZLEM SÜRESİ : **01.10.1966 - 30.09.2006**

ORTALAMA AKIMLAR : **Gözlem süresinde 0.478 m3/sn. (50 Yıllık) 2006 Su yılında 0.737 m3/sn.**

ANLIK EN ÇOK VE EN AZ AKIMLAR:

2006 Su yılında anlık ençok akım	**:**	**10.3**	**m3/sn**	**25.02.2006**
2006 Su yılında anlık enaz akım	**:**	**0.000**	**m3/sn**	**21.10.2005**
Gözlem süresinde anlık ençok akım	**:**	**64.0**	**m3/sn**	**08.06.1972**
Gözlem süresinde anlık enaz akım	**:**	**0.000**	**m3/sn**	**14.07.1986**

9. Anahtar Eğrisi (Seviyeler cm olarak)

Seviye	Akım	Seviye	Akım	Seviye	Akım	Seviye	Akım
1	0.008	12	0.323	35	1.1	142	4.4
3	0.027	16	0.483	50	1.5	173	5.7
5	0.065	20	0.641	70	2.0	197	7.2
7	0.130	24	0.785	100	2.9	235	10.2
9	0.195	28	0.904	119	3.4	260	13.2

Akımlar 01 Ekim 2005 'den 30 Eylül 2006' a kadar m3/sn olarak

Gün	Ekim	Kasım	Aralık	Ocak	Şubat	Mart	Nisan	Mayıs	Haziran	Temmuz	Ağustos	Eylül
01	0.027	0.016	0.065	0.130	0.162	6.21	1.94	0.747	0.483	0.098	0.027	0.027
02	0.027	0.016	0.065	0.130	0.162	6.34	1.89	0.747	0.443	0.098	0.027	0.027
03	0.027	0.016	0.065	0.130	0.234	7.45	1.85	0.709	0.403	0.065	0.027	0.027
04	0.027	0.027	0.065	0.130	0.234	7.45	1.72	0.675	0.363	0.046	0.027	0.027
05	0.027	0.027	0.065	0.130	0.195	5.07	1.67	0.818	0.403	0.065	0.027	0.027
06	0.027	0.027	0.065	0.234	0.234	4.48	1.56	0.942	0.363	0.065	0.027	0.016
07	0.016	0.027	0.065	0.279	0.234	4.16	1.50	1.50	0.323	0.065	0.027	0.008
08	0.016	0.027	0.065	0.234	0.279	4.48	1.45	1.64	0.323	0.065	0.027	0.016
09	0.016	0.027	0.065	0.195	0.323	4.12	1.40	1.19	0.279	0.065	0.027	0.027
10	0.016	0.027	0.065	0.162	0.323	3.51	1.37	1.01	0.234	0.065	0.027	0.027
11	0.016	0.027	0.065	0.130	0.709	3.13	1.32	0.904	0.323	0.065	0.027	0.027
12	0.016	0.027	0.065	0.130	2.43	2.97	1.24	0.818	0.279	0.065	0.027	0.027
13	0.008	0.016	0.065	0.130	2.94	3.20	1.19	0.851	0.234	0.065	0.027	0.027
14	0.008	0.027	0.065	0.130	2.41	4.48	1.19	0.818	0.234	0.046	0.016	0.027
15	0.008	0.046	0.065	0.130	2.16	4.25	1.72	0.709	0.279	0.046	0.016	0.027
16	0.008	0.046	0.065	0.130	2.01	3.20	1.32	0.747	0.195	0.046	0.016	0.027
17	0.008	0.046	0.065	0.130	1.77	3.17	1.24	0.785	0.195	0.046	0.016	0.027
18	0.016	0.046	0.065	0.130	1.56	3.10	1.13	0.709	0.195	0.046	0.016	0.027
19	0.016	0.046	0.065	0.130	3.40	3.10	1.07	0.641	0.162	0.046	0.027	0.016
20	0.016	0.046	0.065	0.785	4.16	2.63	1.01	0.599	0.162	0.027	0.016	0.016
21	0.016	0.046	0.065	0.878	4.83	2.51	0.980	0.520	0.162	0.027	0.027	0.027
22	0.008	0.065	0.065	0.403	5.11	2.51	1.01	0.443	0.162	0.027	0.016	0.027
23	0.008	0.065	0.046	0.279	4.97	2.63	1.07	0.443	0.162	0.046	0.016	0.027
24	0.008	0.065	0.046	0.234	4.97	2.76	1.04	0.403	0.162	0.046	0.016	0.027
25	0.008	0.065	0.046	0.195	8.23	2.66	0.904	0.403	0.130	0.027	0.016	0.027
26	0.016	0.065	0.046	0.195	8.02	2.60	0.818	0.363	0.130	0.046	0.027	0.027
27	0.016	0.065	0.046	0.195	7.52	2.41	0.818	0.363	0.098	0.027	0.027	0.027
28	0.016	0.098	0.046	0.195	6.06	2.23	0.747	0.363	0.098	0.027	0.027	0.027
29	0.016	0.098	0.065	0.195	-----	2.11	0.785	0.363	0.065	0.027	0.027	0.027
30	0.016	0.065	0.065	0.162	-----	2.03	0.818	0.323	0.098	0.027	0.027	0.027
31	0.016	-----	0.098	0.162	-----	2.01	-----	0.279	-----	0.027	0.027	-----
Maks.	0.027	0.098	0.098	1.35	10.3	9.44	1.98	1.92	0.483	0.195	0.098	0.065
Min.	KURU	KURU	0.027	0.098	0.098	1.98	0.747	0.279	0.008	0.016	KURU	KURU
Ortalama	0.016	0.044	0.062	0.219	2.70	3.64	1.26	0.704	0.238	0.050	0.023	0.025
LT/SN/Km2	0.103	0.285	0.407	1.43	17.6	23.8	8.22	4.60	1.55	0.326	0.153	0.163
AKIM mm.	0.277	0.738	1.09	3.84	42.7	63.7	21.3	12.3	4.03	0.874	0.410	0.422
MİL. M3	0.042	0.113	0.167	0.588	6.54	9.76	3.26	1.89	0.617	0.134	0.063	0.065

SU YILI (2006) YILLIK TOPLAM AKIM 23.24 MİLYON M3 152 MM. 4.8 LT/SN/Km2

12. Sakarya Havzasi

D12A126 MERA Ç. PAZAR YOL AYIRIMI

YERİ : **ANKARA-İSTANBUL KARAYOLUNUN 50.KM SİNDEKI PAZAR YOL AYRIMINDAKI KÖPRÜNÜN 40 M. MENBASIINDADIR**

32°42'2" Doğu - 40°20'2" Kuzey

YAĞIŞ ALANI : **197.20 km2** **YAKLAŞIK KOT : 971 m**

GÖZLEM SÜRESİ : **01.12.1974 - 30.09.2006**

ORTALAMA AKIMLAR : **Gözlem süresinde 2.402 m3/sn. (14 Yıllık) 2006 Su yılında 3.828 m3/sn.**

ANLIK EN ÇOK VE EN AZ AKIMLAR:

2006 Su yılında anlık ençok akım	:	**21.8**	**m3/sn**	**03.03.2006**
2006 Su yılında anlık enaz akım	:	**0.074**	**m3/sn**	**19.05.2006**
Gözlem süresinde anlık ençok akım	:	**44.0**	**m3/sn**	**02.08.2001**
Gözlem süresinde anlık enaz akım	:	**0.001**	**m3/sn**	**11.08.1978**

İstasyon için kullanılmış anahtar bulunamadı.

Akımlar 01 Ekim 2005 'den 30 Eylül 2006' a kadar m3/sn olarak

Gün	Ekim	Kasım	Aralık	Ocak	Şubat	Mart	Nisan	Mayıs	Haziran	Temmuz	Ağustos	Eylül
01	6.00	5.62	0.243	0.194	6.60	7.60	0.919	0.121	6.00	5.81	6.00	5.43
02	6.00	5.43	0.243	0.194	6.60	10.4	0.836	0.121	6.00	5.81	6.00	5.43
03	6.00	5.43	0.243	0.194	6.60	14.5	0.753	0.121	6.00	5.81	6.20	5.43
04	6.00	5.43	0.243	0.194	6.60	8.00	1.17	0.121	6.00	5.81	6.20	5.43
05	6.00	5.43	0.243	0.194	6.60	7.00	0.614	0.098	6.00	6.00	6.20	5.43
06	6.00	5.43	0.243	0.292	6.60	7.00	0.558	0.098	6.00	6.00	6.20	5.43
07	6.00	5.43	0.243	0.341	6.60	7.00	0.502	0.098	5.81	6.00	6.20	4.86
08	6.00	5.43	0.243	0.292	6.60	7.20	0.502	0.098	5.81	6.00	6.20	4.86
09	5.81	5.43	0.243	0.194	6.40	7.00	0.502	0.121	5.81	6.00	6.00	4.86
10	5.81	5.24	0.243	0.145	6.40	6.20	0.446	0.098	5.81	6.00	6.00	4.86
11	5.81	1.50	0.243	0.145	6.60	5.81	0.390	0.098	6.00	5.62	6.00	4.86
12	5.81	0.243	0.194	0.145	6.60	5.81	0.341	0.098	5.81	5.62	6.00	4.86
13	5.81	0.243	0.194	0.121	6.60	4.48	0.292	0.098	5.81	5.62	6.00	4.86
14	5.81	0.243	0.194	0.121	6.40	2.05	0.341	0.121	6.00	5.62	6.00	4.86
15	5.81	0.243	0.194	0.145	6.40	1.94	0.243	0.098	6.00	5.62	6.00	4.86
16	5.81	0.243	0.194	0.145	6.40	1.42	0.243	0.098	6.00	5.62	6.00	4.67
17	5.62	0.243	0.194	1.17	6.40	1.33	0.194	0.098	5.81	5.62	6.00	4.67
18	5.62	0.243	0.194	6.20	6.40	1.09	0.194	0.098	5.81	5.62	6.00	4.67
19	5.62	0.243	0.194	6.20	6.40	0.919	0.145	0.098	5.81	5.62	5.81	4.67
20	5.62	0.292	0.243	6.60	6.40	0.753	0.145	0.074	6.00	5.62	5.81	4.67
21	5.62	0.390	0.243	6.60	6.80	0.670	0.145	0.074	5.81	5.81	5.81	4.67
22	5.62	0.243	0.243	6.60	7.20	0.836	0.145	0.074	5.81	5.81	5.81	4.67
23	5.62	0.243	0.243	6.60	7.20	1.61	0.145	0.074	5.81	5.81	5.81	4.67
24	5.62	0.243	0.194	6.60	6.80	2.27	0.121	0.753	5.81	5.81	5.81	4.67
25	5.62	0.243	0.194	6.60	8.00	1.72	0.121	6.00	5.81	5.81	5.81	4.67
26	5.62	0.243	0.194	6.60	8.00	1.42	0.121	6.00	5.81	5.81	5.43	4.67
27	5.62	0.243	0.194	6.60	9.20	1.25	0.121	6.00	5.81	5.81	5.43	4.67
28	5.62	0.243	0.194	6.60	9.44	1.17	0.121	6.00	5.81	5.81	5.43	4.67
29	5.62	0.243	0.194	6.60	-----	1.09	0.121	6.00	5.81	6.00	5.43	4.67
30	5.62	0.243	0.194	6.60	-----	1.00	0.121	6.00	5.81	6.00	5.43	4.67
31	5.62	-----	0.194	6.60	-----	1.17	-----	6.00	-----	6.00	5.43	-----
Maks.	6.20	5.62	0.292	6.80	9.44	21.8	1.17	6.40	6.00	6.40	6.40	5.43
Min.	5.43	0.243	0.145	0.121	6.40	0.670	0.121	0.074	5.62	5.62	5.43	4.67
Ortalama	5.77	2.02	0.218	3.09	6.89	3.93	0.354	1.45	5.88	5.80	5.89	4.88
LT/SN/Km2	29.2	10.2	1.10	15.7	34.9	19.9	1.79	7.37	29.8	29.4	29.8	24.7
AKIM mm.	78.3	26.6	2.96	42.0	84.5	53.3	4.65	19.7	77.3	78.8	79.9	64.1
MİL. M3	15.4	5.24	0.583	8.28	16.7	10.5	0.917	3.89	15.2	15.5	15.8	12.6

SU YILI (2006) YILLIK TOPLAM AKIM 120.61 MİLYON M3 612 MM. 19.4 LT/SN/Km2

12. Sakarya Havzasi

D12A128 OVA Ç. DERİVASYON KANALI

YERİ : **ANKARA İSTANBUL YOLUNUN 40.KM SİNDEKİ KAZAN İLÇESİNİN 20 KM UZAĞINDAKİ REGÜLATÖRÜN MANSABINDADIR.**
32°51'45" Doğu - 40°14'41" Kuzey

YAĞIŞ ALANI : **1000.00 km2** **YAKLAŞIK KOT : 974 m**

GÖZLEM SÜRESİ : **01.03.1974 - 30.09.2006**

ORTALAMA AKIMLAR : **Gözlem süresinde 1.131 m3/sn. (8 Yıllık) 2006 Su yılında 1.116 m3/sn.**

ANLIK EN ÇOK VE EN AZ AKIMLAR:

2006 Su yılında anlık ençok akım	:	**10.2**	**m3/sn**	**30.03.2006**
2006 Su yılında anlık enaz akım	:	**0.000**	**m3/sn**	**01.10.2005**
Gözlem süresinde anlık ençok akım	:	**13.5**	**m3/sn**	**03.04.1975**
Gözlem süresinde anlık enaz akım	:	**0.000**	**m3/sn**	**01.10.1974**

İstasyon için kullanılmış anahtar bulunamadı.

Akımlar 01 Ekim 2005 'den 30 Eylül 2006' a kadar m3/sn olarak

Gün	Ekim	Kasım	Aralık	Ocak	Şubat	Mart	Nisan	Mayıs	Haziran	Temmuz	Ağustos	Eylül
01	KURU	0.264	0.316	0.316	0.170	2.09	9.55	0.950	KURU	KURU	KURU	KURU
02	KURU	0.264	0.316	0.316	0.170	2.68	9.46	0.908	KURU	KURU	KURU	KURU
03	KURU	0.264	0.316	0.342	0.170	6.50	9.10	0.908	KURU	KURU	KURU	KURU
04	KURU	0.264	0.290	0.370	0.190	5.86	8.65	0.908	KURU	KURU	KURU	KURU
05	KURU	0.264	0.290	0.400	0.214	4.27	8.20	0.908	KURU	KURU	KURU	KURU
06	KURU	0.264	0.290	0.432	0.264	5.06	7.93	0.908	KURU	KURU	KURU	KURU
07	KURU	0.264	0.290	0.528	0.290	5.62	7.84	1.17	KURU	KURU	KURU	KURU
08	KURU	0.190	0.264	0.560	0.316	6.34	8.20	1.17	KURU	KURU	KURU	KURU
09	KURU	0.190	0.290	0.496	0.342	6.98	8.11	0.950	KURU	KURU	KURU	KURU
10	KURU	0.190	0.290	0.432	0.316	4.55	7.30	0.950	KURU	KURU	KURU	KURU
11	KURU	0.190	0.290	0.432	0.528	4.06	6.82	0.950	KURU	KURU	KURU	KURU
12	KURU	0.214	0.290	0.400	0.528	3.57	6.18	0.908	KURU	KURU	KURU	KURU
13	KURU	0.190	0.290	0.370	0.400	4.83	5.94	0.908	KURU	KURU	KURU	KURU
14	KURU	0.190	0.264	0.342	0.342	5.46	5.30	0.908	KURU	KURU	KURU	KURU
15	KURU	0.190	0.238	0.290	0.342	5.38	5.54	0.824	KURU	KURU	KURU	KURU
16	KURU	0.214	0.264	0.238	0.264	4.55	4.69	0.740	KURU	KURU	KURU	KURU
17	KURU	0.214	0.316	0.214	0.290	4.69	3.92	0.740	KURU	KURU	KURU	KURU
18	KURU	0.214	0.290	0.238	0.400	4.20	3.43	0.740	KURU	KURU	KURU	KURU
19	KURU	0.214	0.342	0.190	0.432	3.78	3.01	0.668	KURU	KURU	KURU	KURU
20	KURU	0.316	0.432	0.238	0.432	3.36	2.80	0.596	KURU	KURU	KURU	KURU
21	KURU	0.950	0.264	0.290	0.496	3.99	2.56	0.528	KURU	KURU	KURU	KURU
22	KURU	0.740	0.214	0.264	0.632	5.22	2.68	0.528	KURU	KURU	KURU	KURU
23	KURU	0.496	0.342	0.290	0.866	8.74	2.44	0.400	KURU	KURU	KURU	KURU
24	KURU	0.464	0.290	0.214	1.40	9.82	2.20	0.110	KURU	KURU	KURU	KURU
25	KURU	0.432	0.214	0.238	1.45	9.64	1.93	0.001	KURU	KURU	KURU	KURU
26	0.078	0.432	0.290	0.238	2.20	9.46	1.82	0.001	KURU	KURU	KURU	0.063
27	0.078	0.400	0.264	0.170	3.08	9.37	1.71	0.001	KURU	KURU	KURU	0.063
28	0.148	0.400	0.264	0.170	2.15	9.46	1.60	0.001	KURU	KURU	KURU	0.063
29	0.148	0.400	0.264	0.170	-----	9.55	1.35	0.003	KURU	KURU	KURU	0.063
30	0.264	0.370	0.290	0.170	-----	9.55	1.17	KURU	KURU	KURU	KURU	0.078
31	0.264	-----	0.290	0.170	-----	9.73	-----	KURU	-----	KURU	KURU	-----
Maks.	0.264	1.04	0.496	0.596	3.64	10.2	9.91	1.31	KURU	KURU	KURU	0.238
Min.	KURU	0.190	0.110	0.130	0.170	1.93	0.866	KURU	KURU	KURU	KURU	KURU
Ortalama	0.032	0.322	0.289	0.307	0.667	6.08	5.05	0.622	KURU	KURU	KURU	0.011
LT/SN/Km2	0.032	0.322	0.289	0.307	0.667	6.08	5.05	0.622	0.000	0.000	0.000	0.011
AKIM mm.	0.085	0.834	0.774	0.823	1.61	16.3	13.1	1.67	0.000	0.000	0.000	0.029
MİL. M3	0.085	0.834	0.774	0.823	1.61	16.3	13.1	1.67	0.000	0.000	0.000	0.029

SU YILI (2006) YILLIK TOPLAM AKIM 35.23 MİLYON M3 35 MM. 1.1 LT/SN/Km2

12. Sakarya Havzasi

D12A129 ÇUBUK ÇAYI YENİCE (ESENBOĞA)

YERİ : **ANKARA ÇUBUK YOLUNDA ESENBOĞA BELDESİNİN 1 KM MANSABINDA YER ALMAKTADIR.**
32°58'28" Doğu - 40°7'37" Kuzey

YAĞIŞ ALANI : **824.00 km2** **YAKLAŞIK KOT : 935 m**

GÖZLEM SÜRESİ : **22.10.1974 - 30.09.2006**

ORTALAMA AKIMLAR : **Gözlem süresinde 1.551 m3/sn. (15 Yıllık) 2006 Su yılında 0.315 m3/sn.**

ANLIK EN ÇOK VE EN AZ AKIMLAR:

2006 Su yılında anlık ençok akım	**:**	**7.93**	**m3/sn**	**04.03.2006**
2006 Su yılında anlık enaz akım	**:**	**0.001**	**m3/sn**	**28.08.2006**
Gözlem süresinde anlık ençok akım	**:**	**44.0**	**m3/sn**	**14.03.1981**
Gözlem süresinde anlık enaz akım	**:**	**0.000**	**m3/sn**	**13.08.1976**

İstasyon için kullanılmış anahtar bulunamadı.

Akımlar 01 Ekim 2005 'den 30 Eylül 2006' a kadar m3/sn olarak

Gün	Ekim	Kasım	Aralık	Ocak	Şubat	Mart	Nisan	Mayıs	Haziran	Temmuz	Ağustos	Eylül
01	0.060	0.210	0.210	0.355	0.015	1.37	0.788	0.590	0.210	0.170	0.046	0.001
02	0.060	0.210	0.210	0.170	0.015	2.20	0.788	0.590	0.170	0.135	0.046	0.001
03	0.135	0.210	0.210	0.250	0.015	3.05	0.710	0.650	0.135	0.135	0.046	0.001
04	0.105	0.170	0.210	0.250	0.015	3.74	0.710	0.590	0.135	0.080	0.046	0.001
05	0.080	0.170	0.250	0.300	0.015	1.64	0.710	0.590	0.135	0.060	0.046	0.001
06	0.080	0.170	0.250	0.355	0.032	1.37	0.590	0.590	0.135	0.060	0.060	0.001
07	0.080	0.210	0.300	0.300	0.080	1.37	0.590	0.650	0.135	0.032	0.046	0.001
08	0.080	0.170	0.300	0.300	0.105	1.28	0.590	0.650	0.135	0.032	0.046	0.001
09	0.080	0.210	0.300	0.250	0.470	1.91	0.590	0.530	0.105	0.046	0.032	0.001
10	0.080	0.210	0.210	0.300	0.470	1.37	0.590	0.530	0.135	0.060	0.015	0.001
11	0.080	0.250	0.210	0.250	0.590	1.02	0.590	0.530	0.170	0.060	0.015	0.001
12	0.105	0.210	0.210	0.250	0.650	0.944	0.530	0.530	0.170	0.032	0.022	0.001
13	0.080	0.210	0.210	0.210	0.410	0.866	0.530	0.530	0.105	0.046	0.010	0.001
14	0.105	0.210	0.210	0.250	0.410	1.28	0.530	0.530	0.250	0.022	0.015	0.001
15	0.105	0.135	0.250	0.250	0.300	1.28	0.710	0.470	0.250	0.032	0.015	0.001
16	0.105	0.170	0.250	0.210	0.250	1.02	0.590	0.470	0.170	0.032	0.015	0.001
17	0.105	0.135	0.410	0.105	0.250	1.10	0.530	0.470	0.210	0.046	0.022	0.001
18	0.105	0.170	0.355	0.060	0.250	1.02	0.530	0.470	0.170	0.046	0.022	0.001
19	0.105	0.210	0.410	0.046	0.300	1.19	0.530	0.410	0.170	0.032	0.032	0.001
20	0.105	0.210	0.410	0.046	0.530	1.10	0.470	0.410	0.105	0.032	0.032	0.001
21	0.105	0.250	0.300	0.032	0.530	1.02	0.470	0.355	0.105	0.032	0.022	0.001
22	0.105	0.170	0.250	0.015	0.590	1.02	0.530	0.410	0.135	0.060	0.032	0.001
23	0.135	0.135	0.250	0.015	0.650	1.02	0.590	0.355	0.105	0.046	0.007	0.001
24	0.170	0.135	0.210	0.015	0.788	1.10	0.530	0.300	0.105	0.060	0.003	0.001
25	0.135	0.170	0.170	0.015	0.866	1.10	0.470	0.250	0.080	0.046	0.002	0.001
26	0.105	0.135	0.135	0.015	1.46	1.10	0.470	0.250	0.060	0.046	0.002	0.001
27	0.135	0.170	0.060	0.015	2.50	1.02	0.530	0.250	0.060	0.060	0.002	0.001
28	0.170	0.210	0.170	0.015	1.64	0.866	0.530	0.250	0.080	0.032	0.001	0.001
29	0.170	0.170	0.355	0.015	-----	0.866	0.530	0.210	0.060	0.046	0.001	0.001
30	0.210	0.170	0.355	0.015	-----	0.866	0.710	0.210	0.170	0.046	0.001	0.001
31	0.210	-----	0.355	0.015	-----	0.866	-----	0.170	-----	0.046	0.001	-----
Maks.	0.250	0.355	0.470	0.470	3.17	7.93	0.866	0.650	0.300	0.355	0.105	0.001
Min.	0.032	0.105	0.032	0.010	0.015	0.788	0.470	0.135	0.022	0.007	0.001	0.001
Ortalama	0.113	0.185	0.258	0.151	0.507	1.32	0.585	0.445	0.139	0.055	0.023	0.001
LT/SN/Km2	0.137	0.225	0.313	0.184	0.615	1.60	0.710	0.540	0.168	0.067	0.028	0.001
AKIM mm.	0.366	0.584	0.837	0.492	1.49	4.30	1.84	1.45	0.436	0.179	0.074	0.003
MİL. M3	0.302	0.481	0.690	0.405	1.23	3.54	1.52	1.19	0.359	0.148	0.061	0.003

SU YILI (2006) YILLIK TOPLAM AKIM 9.93 MİLYON M3 12 MM. 0.4 LT/SN/Km2

12. Sakarya Havzasi

D12A135 CERRAH D. CERRAH

YERİ : **BURSA-İNEGÖL İLÇESİNİN CERRAH NAHİYESİNİN DAĞ YOLU ÇIKIŞINDABULUNAN BETON KÖPRÜNÜN 50 M. MANSABINDA SAĞ SAHİLDEDİR.**
29°26'0" Doğu - 40°4'0" Kuzey

YAĞIŞ ALANI : **116,13 km2** **YAKLAŞIK KOT : 327 m**

GÖZLEM SÜRESİ : **01.10.1977 - 30.09.2006**

ORTALAMA AKIMLAR : **Gözlem süresinde 2.799 m3/sn. (26 Yıllık) 2006 Su yılında 2.701 m3/sn.**

ANLIK EN ÇOK VE EN AZ AKIMLAR:

2006 Su yılında anlık ençok akım	**:**	**37.2**	**m3/sn**	**03.03.2006**
2006 Su yılında anlık enaz akım	**:**	**0.025**	**m3/sn**	**01.10.2005**
Gözlem süresinde anlık ençok akım	**:**	**90.0**	**m3/sn**	**30.01.1987**
Gözlem süresinde anlık enaz akım	**:**	**0.000**	**m3/sn**	**05.08.1985**

İstasyon için kullanılmış anahtar bulunamadı.

Akımlar 01 Ekim 2005 'den 30 Eylül 2006' a kadar m3/sn olarak

Gün	Ekim	Kasım	Aralık	Ocak	Şubat	Mart	Nisan	Mayıs	Haziran	Temmuz	Ağustos	Eylül
01	0.025	0.096	3.94	6.45	1.15	7.92	4.85	5.78	6.12	1.67	0.042	0.042
02	0.025	0.067	3.18	4.54	1.31	8.31	4.54	5.45	6.12	1.31	0.042	0.096
03	0.331	0.096	3.18	3.43	1.31	20.7	4.54	5.45	6.12	1.00	0.042	0.067
04	0.270	0.096	2.92	2.92	1.31	6.45	4.54	4.24	6.12	0.765	0.042	0.067
05	0.270	0.174	2.67	2.47	1.31	4.54	4.85	3.94	5.15	0.579	0.042	0.067
06	0.219	0.219	2.47	2.47	1.87	4.54	4.85	3.94	4.24	0.477	0.042	0.042
07	0.132	0.219	2.67	2.47	1.67	7.12	5.45	3.69	3.43	0.393	0.042	0.025
08	0.219	0.219	1.87	2.47	1.67	6.12	5.78	4.54	3.18	0.331	0.067	0.025
09	0.096	0.219	2.07	2.27	1.67	5.15	6.12	3.94	3.69	0.270	0.042	0.025
10	0.042	0.132	1.87	2.07	5.15	4.24	6.12	3.69	3.18	0.219	0.042	0.025
11	0.067	0.132	1.87	1.87	9.91	4.85	6.45	3.94	2.92	0.174	0.042	0.025
12	0.096	0.132	1.67	1.49	4.85	10.3	7.52	4.54	2.67	0.132	0.025	0.025
13	0.096	0.174	1.49	1.49	3.69	7.92	10.7	4.85	2.67	0.132	0.025	0.025
14	0.132	0.174	1.49	1.31	3.18	6.79	10.3	4.54	2.92	0.132	0.025	0.025
15	0.132	0.331	1.49	1.15	2.67	5.78	9.11	5.15	2.47	0.132	0.025	0.025
16	0.132	0.393	1.67	1.15	2.67	4.85	8.31	5.15	2.67	0.132	0.025	0.025
17	0.174	0.331	1.87	1.15	2.27	4.24	7.92	5.15	2.47	0.132	0.025	0.025
18	0.132	0.870	2.07	1.15	4.54	3.94	7.92	5.15	2.92	0.132	0.025	0.025
19	0.096	1.87	5.45	3.18	5.15	3.69	7.92	5.15	3.43	0.132	0.025	0.042
20	0.067	5.45	3.18	2.67	6.12	3.18	8.71	5.15	3.18	0.132	0.025	0.096
21	0.042	3.43	2.47	2.07	5.45	2.67	8.71	6.12	2.92	0.132	0.025	0.270
22	0.042	1.87	2.07	1.67	4.85	2.47	8.31	7.12	2.92	0.096	0.025	0.270
23	0.025	1.49	1.87	1.67	4.85	3.43	7.52	7.12	2.47	0.096	0.025	0.096
24	0.025	2.27	1.67	1.49	4.85	4.85	7.52	6.79	2.47	0.096	0.025	0.096
25	0.025	5.78	1.49	1.49	7.52	4.85	6.79	6.79	2.27	0.067	0.025	0.174
26	0.096	7.12	1.49	1.31	10.7	3.94	6.12	7.12	2.07	0.096	0.025	0.132
27	0.132	9.91	1.67	1.31	9.51	3.94	5.78	6.45	2.07	0.067	0.025	0.132
28	0.042	7.92	2.27	1.15	7.92	3.94	5.78	5.45	2.67	0.067	0.025	0.132
29	0.025	6.12	3.18	1.00	-----	3.94	5.78	5.45	2.67	0.067	0.025	0.132
30	0.042	5.78	2.92	1.00	-----	4.54	5.78	5.78	2.47	0.067	0.025	0.579
31	0.096	-----	9.91	1.00	-----	5.15	-----	6.45	-----	0.042	0.025	-----
Maks.	0.870	12.4	17.6	11.1	19.7	37.2	12.4	8.31	6.79	2.27	0.067	1.31
Min.	0.025	0.067	1.31	0.765	1.00	1.87	4.24	3.43	1.49	0.042	0.025	0.025
Ortalama	0.108	2.10	2.58	2.04	4.25	5.62	6.82	5.29	3.36	0.299	0.032	0.094
LT/SN/Km2	0.929	18.1	22.2	17.6	36.6	48.4	58.7	45.6	28.9	2.57	0.274	0.813
AKIM mm.	2.49	46.9	59.6	47.1	88.6	130.	152.	122.	74.9	6.90	0.734	2.11
MİL. M3	0.289	5.45	6.92	5.47	10.3	15.1	17.7	14.2	8.70	0.801	0.085	0.245

SU YILI (2006) YILLIK TOPLAM AKIM 85.26 MİLYON M3 734 MM. 23.3 LT/SN/Km2

12. Sakarya Havzasi

D12A136 MUDURNU Ç. GEBEŞ

YERİ : **ADAPAZARI HENDEK YOLUNUN 9.KMSİNDEN SAĞA AYRILAN HAM YOLUN6.KMSİNDEKİ GEBEŞ KÖYÜNDEDİR**

30°32'0" Doğu - 40°45'0" Kuzey

YAĞIŞ ALANI : **1521.00 km2** **YAKLAŞIK KOT : 25 m**

GÖZLEM SÜRESİ : **01.10.1977 - 30.09.2006**

ORTALAMA AKIMLAR : **Gözlem süresinde 15.942 m3/sn. (9 Yıllık) 2006 Su yılında 15.942 m3/sn.**

ANLIK EN ÇOK VE EN AZ AKIMLAR:

2006 Su yılında anlık ençok akım	:	**133.**	**m3/sn**	**03.03.2006**
2006 Su yılında anlık enaz akım	:	**1.12**	**m3/sn**	**16.08.2006**
Gözlem süresinde anlık ençok akım	:	**227.**	**m3/sn**	**28.02.2004**
Gözlem süresinde anlık enaz akım	:	**0.000**	**m3/sn**	**06.03.1978**

Akımlar 01 Ekim 2005 'den 30 Eylül 2006' a kadar m3/sn olarak

Gün	Ekim	Kasım	Aralık	Ocak	Şubat	Mart	Nisan	Mayıs	Haziran	Temmuz	Ağustos	Eylül
01	3.48	5.76	18.0	25.6	13.5	64.8	37.4	14.0	6.28	6.28	3.00	1.65
02	3.48	5.52	16.0	20.0	14.0	58.4	36.2	13.5	6.28	6.28	3.00	2.09
03	3.64	5.52	16.0	18.0	14.0	87.0	35.6	13.5	6.28	6.28	3.00	2.09
04	3.64	5.52	15.0	16.5	15.0	69.6	34.4	12.4	6.28	6.28	3.00	1.98
05	3.64	9.00	13.5	16.5	15.0	51.3	33.2	12.9	6.00	6.28	3.00	1.98
06	3.64	16.0	12.4	17.5	18.0	48.5	32.0	13.5	6.00	6.28	3.00	2.09
07	3.64	38.0	12.4	21.5	18.5	50.6	31.2	13.5	6.00	6.28	3.00	1.98
08	3.80	22.0	11.8	28.8	17.5	64.8	32.0	12.9	6.00	6.28	3.00	1.87
09	3.80	14.0	11.8	21.0	17.0	56.0	32.0	13.5	6.00	6.28	3.00	1.76
10	3.80	9.92	11.8	18.5	23.0	47.8	30.4	12.9	6.00	6.28	3.00	1.65
11	3.80	8.68	11.8	17.0	61.6	49.9	28.0	12.4	6.00	6.28	3.00	1.76
12	3.80	8.36	10.8	15.5	36.8	71.2	28.0	11.8	6.28	6.28	2.84	1.87
13	4.00	8.36	10.8	16.0	28.0	78.4	28.0	14.5	6.28	4.20	2.84	1.98
14	4.00	8.36	10.8	17.0	23.0	69.6	25.6	13.5	6.28	3.16	2.84	1.87
15	4.20	11.8	10.4	15.5	21.0	63.2	23.5	11.8	6.28	3.16	2.68	1.87
16	4.60	11.3	10.4	14.0	19.5	50.6	22.0	11.8	6.28	3.00	1.76	1.65
17	4.80	8.68	12.4	12.9	18.5	48.5	21.0	11.3	6.28	3.00	1.38	1.56
18	5.04	13.5	11.3	12.4	24.8	43.6	20.0	10.8	6.28	3.00	1.29	1.47
19	5.28	12.4	15.5	15.0	35.6	51.3	19.5	10.4	6.28	3.00	1.20	1.56
20	5.28	32.6	14.0	19.0	48.5	42.9	18.5	9.92	6.28	3.00	1.12	1.76
21	5.04	35.6	12.4	16.5	49.2	41.5	18.0	9.46	6.28	3.00	1.12	3.48
22	4.80	20.0	11.8	16.0	47.8	42.9	17.5	9.00	6.28	3.00	1.12	3.32
23	4.60	17.0	11.3	17.0	49.2	52.8	16.5	9.00	6.28	3.00	1.12	2.52
24	4.60	35.6	11.8	16.0	49.9	57.6	16.5	9.00	6.28	3.00	1.12	3.16
25	4.40	49.2	11.3	15.5	56.0	49.9	16.0	9.00	6.28	3.00	1.12	3.80
26	4.40	64.0	11.3	15.0	77.6	42.2	15.0	9.00	6.28	3.00	1.12	3.48
27	4.20	42.2	12.9	14.5	77.6	39.4	14.5	9.00	6.28	3.00	1.12	2.84
28	4.40	33.2	19.5	14.0	63.2	38.0	14.0	9.00	6.28	3.00	1.12	2.84
29	4.40	25.6	26.4	12.9	-----	38.0	14.0	7.72	6.28	3.00	1.20	3.32
30	5.04	21.5	24.0	12.4	-----	40.1	14.5	6.28	6.28	3.00	1.38	4.40
31	5.52	-----	31.2	12.9	-----	39.4	-----	6.28	-----	3.00	1.20	-----
Maks.	5.76	89.0	40.8	40.1	98.8	133.	40.8	16.0	6.84	6.28	6.28	12.4
Min.	3.48	5.28	10.4	12.4	13.5	36.8	14.0	4.00	6.00	2.84	1.12	1.47
Ortalama	4.28	20.0	14.2	16.8	34.0	53.2	24.2	11.1	6.21	4.32	2.05	2.32
LT/SN/Km2	2.82	13.1	9.35	11.0	22.4	35.0	15.9	7.29	4.09	2.84	1.35	1.53
AKIM mm.	7.54	34.0	25.0	29.6	54.2	93.7	41.2	19.5	10.6	7.61	3.62	3.96
MİL. M3	11.5	51.8	38.1	45.0	82.4	143.	62.6	29.7	16.1	11.6	5.50	6.02

SU YILI (2006) YILLIK TOPLAM AKIM 503.32 MİLYON M3 331 MM. 10.5 LT/SN/Km2

12. Sakarya Havzasi

D12A138 SIRÇASARAY SUYU YEŞİLÖZ

YERİ : POLATLI'DAN DEVLET ÜRETME ÇİFTLİĞİNE GİDEN YOLUN 74.KM SİNDEKİ YEŞİLÖZ KÖPRÜSÜNÜN MANSABINDADIR.
32°20'13" Doğu - 39°8'39" Kuzey

YAĞIŞ ALANI : 294.50 km2 **YAKLAŞIK KOT** : 856 m

GÖZLEM SÜRESİ : 15.10.1976 - 30.09.2006

ORTALAMA AKIMLAR : Gözlem süresinde 0.281 m3/sn. (26 Yıllık) 2006 Su yılında 0.029 m3/sn.

ANLIK EN ÇOK VE EN AZ AKIMLAR:

2006 Su yılında anlık ençok akım	:	4.13	m3/sn	29.06.2006
2006 Su yılında anlık enaz akım	:	0.000	m3/sn	01.10.2005
Gözlem süresinde anlık ençok akım	:	118.	m3/sn	02.08.2001
Gözlem süresinde anlık enaz akım	:	0.000	m3/sn	01.09.1987

7. Anahtar Eğrisi (Seviyeler cm olarak)

Seviye	Akım	Seviye	Akım	Seviye	Akım	Seviye	Akım
1	0.000	16	0.420	100	34.3	190	98.0
4	0.000	19	0.740	130	54.0	200	106.
7	0.013	30	3.0	160	75.0	210	114.
10	0.064	45	7.5	170	82.0	220	122.
13	0.192	70	17.8	180	90.0		

Akımlar 01 Ekim 2005 'den 30 Eylül 2006' a kadar m3/sn olarak

Gün	Ekim	Kasım	Aralık	Ocak	Şubat	Mart	Nisan	Mayıs	Haziran	Temmuz	Ağustos	Eylül
01	KURU	KURU	KURU	0.006	0.013	0.145	0.064	0.064	KURU	0.024	KURU	KURU
02	KURU	KURU	KURU	0.006	0.013	0.145	0.064	0.098	KURU	0.024	KURU	KURU
03	0.145	KURU	KURU	0.006	0.013	0.145	0.064	0.098	KURU	0.024	KURU	KURU
04	0.002	0.002	KURU	0.006	0.013	0.145	0.098	0.098	KURU	0.024	KURU	KURU
05	KURU	KURU	KURU	0.006	0.013	0.145	0.098	0.098	KURU	0.024	KURU	KURU
06	KURU	KURU	KURU	0.006	0.013	0.145	0.064	0.098	0.006	0.024	KURU	KURU
07	KURU	KURU	KURU	0.006	0.024	0.145	0.024	0.145	KURU	0.024	KURU	KURU
08	KURU	KURU	KURU	0.006	0.024	0.098	0.024	0.098	KURU	0.024	KURU	KURU
09	KURU	KURU	KURU	0.006	0.024	0.145	0.013	0.098	KURU	KURU	KURU	KURU
10	KURU	KURU	KURU	0.006	0.064	0.145	0.013	0.098	KURU	KURU	KURU	KURU
11	KURU	KURU	0.002	0.006	0.064	0.145	0.013	0.098	0.013	KURU	KURU	KURU
12	KURU	KURU	0.002	0.006	0.064	0.098	KURU	0.098	0.013	KURU	KURU	KURU
13	KURU	KURU	0.002	0.006	0.064	0.145	KURU	0.064	0.013	KURU	KURU	KURU
14	KURU	KURU	0.002	0.006	0.064	0.098	KURU	0.064	0.024	KURU	KURU	KURU
15	KURU	KURU	0.002	0.006	0.064	0.098	KURU	0.064	0.024	KURU	KURU	KURU
16	KURU	KURU	0.006	0.006	0.064	0.098	KURU	0.064	0.024	KURU	KURU	KURU
17	KURU	KURU	0.006	0.006	0.064	0.098	KURU	0.064	0.024	KURU	KURU	KURU
18	KURU	KURU	0.006	0.006	0.064	0.145	KURU	0.064	0.024	KURU	KURU	KURU
19	KURU	KURU	0.006	0.006	0.064	0.145	KURU	0.064	0.013	KURU	KURU	KURU
20	KURU	KURU	0.006	0.006	0.064	0.145	KURU	0.064	0.006	KURU	KURU	KURU
21	KURU	KURU	0.006	0.013	0.064	0.145	KURU	0.064	KURU	KURU	KURU	KURU
22	KURU	KURU	0.006	0.013	0.255	0.145	KURU	0.024	KURU	KURU	KURU	KURU
23	KURU	KURU	0.006	0.013	0.420	0.145	0.006	0.024	KURU	KURU	KURU	KURU
24	KURU	KURU	0.006	0.013	0.420	0.098	0.064	0.024	KURU	KURU	KURU	KURU
25	KURU	KURU	0.006	0.013	0.340	0.098	0.064	0.024	KURU	KURU	0.002	KURU
26	KURU	KURU	0.006	0.013	0.192	0.098	0.040	KURU	KURU	KURU	KURU	KURU
27	KURU	KURU	0.006	0.013	0.255	0.098	0.006	KURU	KURU	KURU	KURU	KURU
28	KURU	KURU	0.006	0.013	0.255	0.098	0.013	KURU	0.002	KURU	KURU	KURU
29	KURU	KURU	0.006	0.013	-----	0.098	0.024	KURU	0.192	KURU	KURU	KURU
30	KURU	KURU	0.006	0.013	-----	0.098	0.040	KURU	0.098	KURU	KURU	KURU
31	KURU	-----	0.006	0.013	-----	0.098	-----	KURU	-----	KURU	KURU	-----
Maks.	3.05	0.024	0.006	0.024	0.740	0.255	0.420	0.192	4.13	0.340	0.040	KURU
Min.	KURU	KURU	KURU	0.002	0.013	0.098	KURU	KURU	KURU	KURU	KURU	KURU
Ortalama	0.005	0.000	0.003	0.008	0.109	0.124	0.027	0.060	0.016	0.006	0.000	KURU
LT/SN/Km2	0.016	0.000	0.012	0.029	0.370	0.420	0.090	0.204	0.054	0.021	0.000	0.000
AKIM mm.	0.043	0.001	0.031	0.077	0.896	1.13	0.234	0.546	0.140	0.056	0.001	0.000
MİL. M3	0.013	0.000	0.009	0.023	0.264	0.332	0.069	0.161	0.041	0.017	0.000	0.000

SU YILI (2006) YILLIK TOPLAM AKIM 0.93 MİLYON M3 3 MM. 0.1 LT/SN/Km2

12. Sakarya Havzasi

D12A146 GÖYNÜK S. YENİKÖY

YERİ : **ADAPAZARI GEYVE TARAKLI NAHİYESİNİN 4 5KM BATISINDAKİ GÖYNÜKYOLUNUN 200MT DEKİ İĞDELİ KÖYÜNÜN 7 KM MANSABINDADIR.**
30°32'0" Doğu - 40°24'0" Kuzey

YAĞIŞ ALANI : **363.50 km2** **YAKLAŞIK KOT : 425 m**

GÖZLEM SÜRESİ : **01.10.1978 - 30.09.2006**

ORTALAMA AKIMLAR : **Gözlem süresinde 2.116 m3/sn. (27 Yıllık) 2006 Su yılında 1.826 m3/sn.**

ANLIK EN ÇOK VE EN AZ AKIMLAR:

2006 Su yılında anlık ençok akım	**:**	**13.8**	**m3/sn**	**29.05.2006**
2006 Su yılında anlık enaz akım	**:**	**0.035**	**m3/sn**	**24.10.2005**
Gözlem süresinde anlık ençok akım	**:**	**190.**	**m3/sn**	**07.07.1991**
Gözlem süresinde anlık enaz akım	**:**	**0.000**	**m3/sn**	**05.08.1985**

Akımlar 01 Ekim 2005 'den 30 Eylül 2006' a kadar m3/sn olarak

Gün	Ekim	Kasım	Aralık	Ocak	Şubat	Mart	Nisan	Mayıs	Haziran	Temmuz	Ağustos	Eylül
01	2.28	0.564	1.42	1.61	1.42	6.70	5.10	2.76	0.472	0.230	0.110	0.230
02	2.28	0.564	1.42	1.61	1.42	6.70	5.10	2.76	0.472	0.230	0.110	0.380
03	2.28	1.03	1.42	1.80	1.42	7.62	5.10	2.76	0.380	0.320	0.110	0.564
04	1.61	1.80	1.42	1.80	1.42	9.00	5.10	2.76	0.472	0.564	0.110	0.564
05	1.61	2.28	1.42	1.80	1.42	9.00	4.70	2.76	0.472	0.564	0.110	0.564
06	1.42	2.28	1.42	2.04	1.42	8.54	4.70	2.76	0.472	0.564	0.110	0.564
07	1.61	2.28	1.42	2.04	1.61	8.08	4.70	2.76	0.472	0.472	0.110	0.564
08	1.03	2.28	1.42	2.04	1.61	8.08	4.36	2.76	0.380	0.380	0.110	0.564
09	1.22	1.80	1.22	2.04	1.61	8.08	4.36	2.76	0.472	0.320	0.110	0.564
10	1.80	1.61	1.22	2.04	1.61	8.08	4.36	2.76	0.564	0.280	0.110	0.564
11	1.22	1.22	1.22	2.04	2.76	8.08	4.02	2.76	0.564	0.280	0.110	0.656
12	0.840	1.03	1.22	2.04	2.76	8.08	4.02	2.76	0.656	0.230	0.110	0.656
13	0.748	0.748	1.22	2.04	2.52	8.08	4.02	2.76	0.564	0.280	0.110	0.656
14	0.748	0.748	1.22	2.04	1.80	8.08	3.68	2.28	0.564	0.320	0.110	0.656
15	0.748	0.564	1.22	2.04	1.80	8.08	3.68	1.80	0.564	0.320	0.110	0.656
16	0.748	0.472	1.22	1.80	1.42	8.08	3.68	2.04	0.564	0.280	0.110	0.656
17	0.748	0.472	1.22	1.80	1.42	8.08	3.34	2.04	0.564	0.200	0.092	0.656
18	0.748	0.472	1.22	1.61	1.22	8.08	3.34	2.04	0.472	0.200	0.092	0.656
19	0.564	0.656	1.22	1.61	1.22	8.08	3.34	2.04	0.472	0.200	0.092	0.656
20	0.748	0.656	1.22	1.80	1.61	6.70	3.00	1.80	0.472	0.170	0.092	0.748
21	0.380	0.656	1.22	1.80	1.80	5.90	3.00	1.61	0.380	0.170	0.092	0.840
22	0.380	0.656	1.22	1.80	2.76	5.90	3.00	1.80	0.320	0.170	0.092	1.22
23	0.380	0.656	1.22	1.80	3.34	5.90	3.00	1.22	0.320	0.170	0.092	0.840
24	0.280	0.656	1.22	1.42	3.34	5.90	3.00	1.22	0.320	0.170	0.092	0.748
25	0.200	0.656	1.22	1.42	3.68	6.70	2.76	1.22	0.280	0.170	0.092	0.564
26	0.280	1.03	1.22	1.42	4.70	6.70	3.00	0.840	0.280	0.130	0.092	0.564
27	0.320	1.22	1.22	1.42	6.30	6.30	3.00	0.840	0.320	0.130	0.092	0.472
28	0.472	1.42	1.22	1.42	6.70	6.30	3.00	0.840	0.320	0.130	0.092	0.472
29	0.564	1.42	1.22	1.42	-----	5.90	3.00	0.840	0.320	0.130	0.110	0.472
30	0.564	1.42	1.42	1.42	-----	5.50	2.76	0.564	0.320	0.130	0.110	0.564
31	0.564	-----	1.42	1.42	-----	5.50	-----	0.564	-----	0.110	0.110	-----
Maks.	2.28	4.70	1.61	2.52	7.16	9.00	6.70	13.8	0.748	0.656	1.03	2.28
Min.	0.035	0.230	1.03	1.22	1.22	4.70	2.76	0.564	0.230	0.110	0.062	0.230
Ortalama	0.948	1.11	1.28	1.75	2.36	7.28	3.77	1.98	0.442	0.259	0.103	0.618
LT/SN/Km2	2.61	3.06	3.53	4.83	6.50	20.0	10.4	5.46	1.22	0.711	0.283	1.70
AKIM mm.	6.98	7.92	9.46	12.9	15.7	53.7	26.9	14.6	3.15	1.90	0.759	4.40
MİL. M3	2.54	2.88	3.44	4.70	5.71	19.5	9.78	5.31	1.15	0.692	0.276	1.60

SU YILI (2006) YILLIK TOPLAM AKIM 57.58 MİLYON M3 158 MM. 5.0 LT/SN/Km2

12. Sakarya Havzasi

D12A147 PAZAR ÇAYI PAZAR

YERİ : **ANKARA-İSTANBUL YOLUNUN 50.KM SİNDE SAĞA AYRILAN YOLUN 5.KM SİNDE PAZAR NAHİYESİNDEKİ KÖPRÜDEDİR.**
32°45'5" Doğu - 40°19'43" Kuzey

YAĞIŞ ALANI : **56.20 km2** **YAKLAŞIK KOT : 1010 m**

GÖZLEM SÜRESİ : **01.01.1977 - 30.09.2006**

ORTALAMA AKIMLAR : **Gözlem süresinde 0.305 m3/sn. (19 Yıllık) 2006 Su yılında 0.175 m3/sn.**

ANLIK EN ÇOK VE EN AZ AKIMLAR:

2006 Su yılında anlık ençok akım	:	**3.45**	**m3/sn**	**03.03.2006**
2006 Su yılında anlık enaz akım	:	**0.018**	**m3/sn**	**02.10.2005**
Gözlem süresinde anlık ençok akım	:	**38.0**	**m3/sn**	**14.05.1982**
Gözlem süresinde anlık enaz akım	:	**0.000**	**m3/sn**	**06.08.1979**

İstasyon için kullanılmış anahtar bulunamadı.

Akımlar 01 Ekim 2005 'den 30 Eylül 2006' a kadar m3/sn olarak

Gün	Ekim	Kasım	Aralık	Ocak	Şubat	Mart	Nisan	Mayıs	Haziran	Temmuz	Ağustos	Eylül
01	0.036	0.036	0.058	0.058	0.058	1.38	0.732	0.112	0.036	0.036	0.018	0.036
02	0.018	0.036	0.058	0.058	0.058	1.29	0.596	0.112	0.036	0.036	0.018	0.018
03	0.018	0.036	0.058	0.058	0.058	2.44	0.528	0.146	0.036	0.036	0.018	0.018
04	0.018	0.084	0.058	0.058	0.058	1.38	0.460	0.112	0.018	0.036	0.018	0.036
05	0.018	0.084	0.058	0.058	0.058	1.04	0.355	0.084	0.018	0.036	0.018	0.036
06	0.018	0.084	0.058	0.058	0.058	1.29	0.310	0.084	0.018	0.036	0.018	0.036
07	0.018	0.084	0.058	0.036	0.084	1.38	0.310	0.084	0.018	0.036	0.018	0.036
08	0.018	0.084	0.058	0.036	0.058	1.38	0.265	0.112	0.018	0.036	0.018	0.036
09	0.018	0.084	0.058	0.036	0.084	1.38	0.265	0.112	0.036	0.036	0.018	0.036
10	0.018	0.084	0.058	0.036	0.058	0.880	0.220	0.112	0.036	0.036	0.018	0.036
11	0.018	0.084	0.058	0.036	0.220	0.664	0.220	0.112	0.036	0.036	0.036	0.036
12	0.018	0.084	0.058	0.036	0.146	0.800	0.180	0.084	0.084	0.036	0.036	0.036
13	0.036	0.084	0.058	0.036	0.112	1.38	0.180	0.112	0.058	0.036	0.036	0.036
14	0.036	0.084	0.058	0.036	0.112	1.57	0.146	0.112	0.058	0.036	0.036	0.036
15	0.018	0.084	0.058	0.036	0.112	1.29	0.180	0.084	0.084	0.036	0.036	0.036
16	0.018	0.084	0.058	0.036	0.112	0.960	0.146	0.084	0.084	0.036	0.036	0.036
17	0.036	0.058	0.084	0.036	0.146	0.960	0.146	0.084	0.058	0.036	0.036	0.036
18	0.036	0.058	0.084	0.036	0.112	0.732	0.146	0.084	0.058	0.036	0.036	0.018
19	0.036	0.058	0.084	0.036	0.084	0.596	0.146	0.084	0.058	0.036	0.058	0.018
20	0.036	0.058	0.058	0.036	0.112	0.528	0.146	0.084	0.058	0.036	0.058	0.018
21	0.036	0.058	0.058	0.036	0.180	0.664	0.146	0.084	0.058	0.036	0.058	0.018
22	0.036	0.058	0.058	0.036	0.146	1.04	0.146	0.058	0.058	0.036	0.058	0.018
23	0.036	0.058	0.058	0.036	0.146	1.88	0.146	0.058	0.058	0.036	0.058	0.036
24	0.036	0.058	0.058	0.036	0.220	2.20	0.146	0.058	0.058	0.036	0.058	0.058
25	0.036	0.058	0.058	0.036	0.355	1.57	0.146	0.058	0.036	0.036	0.058	0.112
26	0.018	0.058	0.058	0.036	1.29	1.29	0.112	0.058	0.036	0.018	0.036	0.112
27	0.018	0.058	0.058	0.058	1.29	1.12	0.112	0.058	0.036	0.018	0.036	0.084
28	0.018	0.058	0.058	0.058	0.800	1.04	0.112	0.058	0.036	0.018	0.036	0.084
29	0.018	0.058	0.058	0.036	-----	0.960	0.112	0.058	0.036	0.018	0.036	0.084
30	0.018	0.058	0.058	0.058	-----	0.960	0.112	0.058	0.036	0.018	0.018	0.112
31	0.018	-----	0.058	0.058	-----	0.960	-----	0.036	-----	0.018	0.036	-----
Maks.	0.112	0.112	0.084	0.084	2.56	3.45	0.960	0.146	0.112	0.036	0.058	0.146
Min.	0.018	0.036	0.058	0.018	0.036	0.460	0.112	0.036	0.018	0.018	0.018	0.018
Ortalama	0.025	0.067	0.061	0.043	0.226	1.19	0.232	0.085	0.045	0.033	0.035	0.045
LT/SN/Km2	0.444	1.19	1.08	0.767	4.02	21.2	4.13	1.51	0.803	0.579	0.615	0.800
AKIM mm.	1.19	3.09	2.88	2.05	9.73	56.9	10.7	4.05	2.08	1.55	1.65	2.07
MİL. M3	0.067	0.174	0.162	0.115	0.547	3.20	0.602	0.228	0.117	0.087	0.093	0.116

SU YILI (2006) YILLIK TOPLAM AKIM 5.51 MİLYON M3 98 MM. 3.1 LT/SN/Km2

12. Sakarya Havzasi

D12A150 KOCADERE ÖMERKÖY

YERİ : **MİHALLICIK-ÖMERKÖY KOCADERE ÜZERİNDEKİ KÖPRÜNÜN 150.MMENBAINDADIR.EŞELLİ-LİMNİGRAFLI**
31°31'0" Doğu - 39°51'0" Kuzey

YAĞIŞ ALANI : **16.05 km2** **YAKLAŞIK KOT : 1207 m**

GÖZLEM SÜRESİ : **01.10.1978 - 30.09.2006**

ORTALAMA AKIMLAR : **Gözlem süresinde 0.064 m3/sn. (15 Yıllık) 2006 Su yılında 0.013 m3/sn.**

ANLIK EN ÇOK VE EN AZ AKIMLAR:

2006 Su yılında anlık ençok akım	**:**	**0.440 m3/sn**	**03.03.2006**
2006 Su yılında anlık enaz akım	**:**	**0.000 m3/sn**	**06.10.2005**
Gözlem süresinde anlık ençok akım	**:**	**8.60 m3/sn**	**01.04.1984**
Gözlem süresinde anlık enaz akım	**:**	**0.000 m3/sn**	**01.10.1978**

Akımlar 01 Ekim 2005 'den 30 Eylül 2006' a kadar m3/sn olarak

Gün	Ekim	Kasım	Aralık	Ocak	Şubat	Mart	Nisan	Mayıs	Haziran	Temmuz	Ağustos	Eylül
01	0.002	0.002	0.002	0.002	0.002	0.010	0.023	0.023	0.010	0.023	0.010	0.010
02	0.002	0.002	0.002	0.002	0.002	0.023	0.023	0.023	0.010	0.023	0.010	0.010
03	0.002	0.002	0.002	0.002	0.002	0.178	0.023	0.023	0.010	0.023	0.010	0.010
04	0.002	0.002	0.002	0.002	0.002	0.063	0.023	0.023	0.010	0.023	0.010	0.010
05	0.002	0.002	0.002	0.002	0.002	0.063	0.023	0.023	0.010	0.023	0.010	0.010
06	KURU	0.002	0.002	0.002	0.002	0.063	0.023	0.023	0.023	0.023	0.010	0.010
07	KURU	0.002	0.002	0.002	0.002	0.063	0.023	0.023	0.023	0.023	0.010	0.010
08	KURU	0.002	0.002	0.002	0.002	0.063	0.023	0.023	0.023	0.023	0.010	0.010
09	KURU	0.002	0.002	0.002	0.002	0.063	0.023	0.023	0.023	0.023	0.010	0.010
10	0.002	0.002	0.002	0.002	0.002	0.042	0.023	0.023	0.023	0.010	0.010	0.010
11	0.002	KURU	0.002	0.002	0.002	0.042	0.023	0.023	0.023	0.023	0.010	0.010
12	0.002	KURU	0.002	0.002	0.002	0.042	0.023	0.023	0.023	0.023	0.010	0.010
13	0.002	KURU	0.002	0.002	0.002	0.042	0.023	0.023	0.023	0.023	0.010	0.010
14	0.002	KURU	0.002	0.002	0.002	0.042	0.023	0.023	0.023	0.023	0.010	0.010
15	0.002	KURU	KURU	0.002	0.002	0.042	0.023	0.023	0.023	0.023	0.010	0.010
16	0.002	KURU	KURU	0.002	0.002	0.042	0.023	0.023	0.023	0.023	0.023	0.010
17	0.002	KURU	KURU	0.002	0.002	0.042	0.023	0.023	0.023	0.023	0.010	0.010
18	0.002	KURU	KURU	0.002	0.002	0.042	0.023	0.023	0.023	0.010	0.010	0.010
19	0.002	KURU	KURU	0.002	0.010	0.042	0.023	0.023	0.023	0.010	0.010	0.010
20	0.002	KURU	KURU	0.002	0.002	0.042	0.023	0.023	0.023	0.023	0.010	0.010
21	0.002	KURU	KURU	0.002	0.002	0.042	0.023	0.023	0.023	0.023	0.010	0.010
22	0.002	KURU	KURU	0.002	0.002	0.042	0.023	0.023	0.023	0.023	0.010	0.010
23	0.002	0.002	KURU	0.002	0.002	0.042	0.023	0.023	0.023	0.042	0.010	0.010
24	0.002	0.002	KURU	0.002	0.002	0.042	0.023	0.023	0.023	0.023	0.010	0.010
25	0.002	0.002	KURU	0.002	0.002	0.042	0.023	0.023	0.023	0.010	0.010	0.010
26	0.002	0.002	KURU	0.002	0.002	0.042	0.023	0.023	0.023	0.010	0.010	0.010
27	0.002	0.002	KURU	0.002	0.010	0.023	0.023	0.023	0.023	0.010	0.010	0.010
28	0.002	0.002	KURU	0.002	0.010	0.023	0.023	0.023	0.023	0.010	0.010	0.010
29	0.002	0.002	0.002	0.002	-----	0.023	0.023	0.023	0.023	0.010	0.002	0.010
30	0.002	0.002	0.002	0.002	-----	0.023	0.023	0.010	0.023	0.010	0.002	0.010
31	0.002	-----	0.002	0.002	-----	0.023	-----	0.010	-----	0.010	0.002	-----
Maks.	0.002	0.002	0.002	0.002	0.010	0.440	0.063	0.063	0.042	0.063	0.023	0.023
Min.	KURU	KURU	KURU	0.002	0.002	0.010	0.023	0.002	0.010	KURU	0.002	0.010
Ortalama	0.002	0.001	0.001	0.002	0.003	0.046	0.023	0.022	0.021	0.019	0.010	0.010
LT/SN/Km2	0.109	0.075	0.068	0.125	0.178	2.85	1.43	1.38	1.30	1.21	0.601	0.623
AKIM mm.	0.291	0.194	0.183	0.334	0.431	7.63	3.71	3.70	3.36	3.24	1.61	1.61
MİL. M3	0.005	0.003	0.003	0.005	0.007	0.123	0.060	0.059	0.054	0.052	0.026	0.026

SU YILI (2006) YILLIK TOPLAM AKIM 0.42 MİLYON M3 26 MM. 0.8 LT/SN/Km2

12. Sakarya Havzasi

D12A152 KOKAR Ç. BEŞKARİŞ

YERİ : **KÜTAHYA İLİ ALTINTAŞ NAHİYESİ BEŞKARIŞ KÖYÜNDEN 5 KMUZAKLIKTADIR.LİMNIGRAFLI.**
30°9'0" Doğu - 38°58'0" Kuzey

YAĞIŞ ALANI : **214.80 km2** **YAKLAŞIK KOT : 1075 m**

GÖZLEM SÜRESİ : **01.10.1979 - 30.09.2006**

ORTALAMA AKIMLAR : **Gözlem süresinde 0.910 m3/sn. (25 Yıllık) 2006 Su yılında 0.827 m3/sn.**

ANLIK EN ÇOK VE EN AZ AKIMLAR:

2006 Su yılında anlık ençok akım	**:**	**16.0**	**m3/sn**	**04.03.2006**
2006 Su yılında anlık enaz akım	**:**	**0.041**	**m3/sn**	**17.08.2006**
Gözlem süresinde anlık ençok akım	**:**	**53.0**	**m3/sn**	**16.12.1981**
Gözlem süresinde anlık enaz akım	**:**	**0.041**	**m3/sn**	**07.12.2001**

3. Anahtar Eğrisi (Seviyeler cm olarak)

Seviye	Akım	Seviye	Akım	Seviye	Akım	Seviye	Akım
15	0.010	54	0.780	79	3.4	140	17.0
32	0.087	59	1.1	84	4.2	190	32.0
39	0.200	64	1.6	89	5.1	200	36.0
44	0.340	69	2.1	94	5.9	210	39.0
49	0.540	74	2.8	99	6.8	220	43.0

Akımlar 01 Ekim 2005 'den 30 Eylül 2006' a kadar m3/sn olarak

Gün	Ekim	Kasım	Aralık	Ocak	Şubat	Mart	Nisan	Mayıs	Haziran	Temmuz	Ağustos	Eylül
01	0.230	0.260	0.280	0.310	0.380	5.40	1.90	0.910	0.500	0.380	0.230	0.260
02	0.230	0.260	0.280	0.310	0.380	6.60	1.90	0.850	0.500	0.380	0.230	0.260
03	0.230	0.260	0.280	0.310	0.380	5.90	1.80	0.850	0.500	0.380	0.230	0.260
04	0.230	0.260	0.280	0.310	0.380	8.22	1.55	0.850	0.500	0.380	0.230	0.260
05	0.230	0.260	0.280	0.310	0.380	4.20	1.55	0.850	0.500	0.380	0.230	0.260
06	0.230	0.260	0.280	0.310	0.380	3.20	1.55	0.910	0.500	0.380	0.230	0.260
07	0.230	0.260	0.280	0.380	0.380	3.00	1.55	0.910	0.500	0.380	0.230	0.260
08	0.230	0.260	0.280	0.380	0.380	3.10	1.55	1.15	0.500	0.380	0.230	0.260
09	0.230	0.260	0.280	0.340	0.380	3.20	1.55	1.10	0.500	0.380	0.230	0.260
10	0.230	0.260	0.280	0.340	0.380	2.30	1.55	0.910	0.460	0.380	0.230	0.260
11	0.230	0.260	0.280	0.340	0.420	2.30	1.55	0.910	0.460	0.380	0.230	0.260
12	0.230	0.260	0.280	0.310	0.730	3.20	1.35	0.850	0.460	0.380	0.230	0.260
13	0.230	0.260	0.280	0.310	1.70	3.30	1.15	0.780	0.460	0.340	0.230	0.260
14	0.230	0.260	0.280	0.310	1.45	4.30	1.15	0.780	0.460	0.340	0.230	0.260
15	0.230	0.280	0.280	0.310	1.35	5.40	1.20	0.680	0.380	0.340	0.230	0.260
16	0.230	0.280	0.280	0.310	1.35	4.30	1.45	0.680	0.380	0.340	0.230	0.260
17	0.230	0.280	0.280	0.310	1.10	4.30	1.20	0.680	0.380	0.340	0.230	0.260
18	0.230	0.280	0.280	0.310	0.910	3.70	1.15	0.680	0.380	0.340	0.260	0.260
19	0.230	0.280	0.280	0.310	1.20	3.40	1.15	0.680	0.380	0.260	0.260	0.280
20	0.230	0.280	0.280	0.340	3.40	2.30	1.15	0.630	0.380	0.230	0.260	0.260
21	0.230	0.280	0.280	0.540	3.80	2.30	1.15	0.580	0.380	0.230	0.260	0.260
22	0.230	0.280	0.280	0.500	4.00	2.10	1.15	0.580	0.380	0.230	0.260	0.260
23	0.230	0.280	0.280	0.460	3.70	2.20	1.15	0.580	0.380	0.230	0.260	0.260
24	0.260	0.280	0.280	0.420	3.80	2.50	1.15	0.580	0.380	0.230	0.260	0.260
25	0.200	0.280	0.280	0.420	6.50	2.50	1.15	0.540	0.380	0.230	0.260	0.260
26	0.260	0.280	0.280	0.420	7.78	2.50	1.10	0.540	0.380	0.230	0.260	0.260
27	0.260	0.280	0.280	0.380	7.12	2.20	1.00	0.540	0.380	0.230	0.260	0.260
28	0.260	0.280	0.310	0.380	6.30	2.10	1.00	0.500	0.380	0.230	0.260	0.260
29	0.260	0.280	0.310	0.380	-----	2.00	1.00	0.500	0.380	0.230	0.260	0.260
30	0.260	0.280	0.310	0.380	-----	2.00	0.910	0.500	0.380	0.230	0.260	0.260
31	0.260	-----	0.310	0.380	-----	2.00	-----	0.500	-----	0.230	0.260	-----
Maks.	0.380	0.280	1.00	0.580	11.1	16.0	2.00	1.35	0.540	0.580	1.35	0.380
Min.	0.200	0.180	0.280	0.310	0.380	2.00	0.850	0.230	0.380	0.180	0.041	0.260
Ortalama	0.236	0.271	0.284	0.359	2.16	3.42	1.32	0.728	0.429	0.310	0.244	0.261
LT/SN/Km2	1.10	1.26	1.32	1.67	10.0	15.9	6.16	3.39	2.00	1.44	1.13	1.21
AKIM mm.	2.94	3.27	3.54	4.47	24.3	42.6	16.0	9.08	5.18	3.87	3.04	3.15
MİL. M3	0.632	0.702	0.760	0.961	5.22	9.16	3.43	1.95	1.11	0.831	0.652	0.676

SU YILI (2006) YILLIK TOPLAM AKIM 26.08 MİLYON M3 121 MM. 3.9 LT/SN/Km2

12. Sakarya Havzasi

D12A153 GÖKSU N. BOGAZKÖY

YERİ : 1977BURSA-İNEGÖL İLÇESİNDEN YENİŞEHİR İLÇESİNE GİDERKEN 15.KMDE BOĞAZ KÖYÜNÜN 1 KM. MANSABIDA SOL SAHİLDEDİR.
29°32'4" Doğu - 40°11'50" Kuzey

YAĞIŞ ALANI : 1174,30 km2 **YAKLAŞIK KOT :** 245 m

GÖZLEM SÜRESİ : 01.03.1977 – 30.09.2006

ORTALAMA AKIMLAR : Gözlem süresinde 15.227 m3/sn. (25 Yıllık) 2006 Su yılında 15.873 m3/sn.

ANLIK EN ÇOK VE EN AZ AKIMLAR:

2006 Su yılında anlık ençok akım	:	200.	m3/sn	03.03.2006
2006 Su yılında anlık enaz akım	:	1.55	m3/sn	09.08.2006
Gözlem süresinde anlık ençok akım	:	500.	m3/sn	18.10.1989
Gözlem süresinde anlık enaz akım	:	0.000	m3/sn	11.09.1977

İstasyon için kullanılmış anahtar bulunamadı.

Akımlar 01 Ekim 2005 'den 30 Eylül 2006' a kadar m3/sn olarak

Gün	Ekim	Kasım	Aralık	Ocak	Şubat	Mart	Nisan	Mayıs	Haziran	Temmuz	Ağustos	Eylül
01	1.80	3.56	9.44	19.2	18.5	61.6	33.8	20.9	12.4	5.37	1.77	1.55
02	2.03	3.33	9.61	20.3	18.5	55.4	31.6	20.4	12.2	4.49	1.77	1.55
03	2.90	3.33	9.44	18.2	18.5	143.	30.9	19.7	11.9	4.74	1.77	1.55
04	2.41	3.10	9.61	16.9	18.7	97.2	30.6	19.0	11.5	4.61	1.77	1.55
05	2.31	3.79	9.61	16.9	18.7	60.8	30.9	18.7	10.8	4.25	1.77	1.55
06	2.21	5.64	9.61	16.6	16.6	50.9	30.6	18.0	10.1	3.88	1.77	1.55
07	2.11	6.63	9.26	17.3	13.5	48.5	30.6	17.3	9.61	3.63	1.77	1.55
08	2.11	5.78	8.92	16.6	12.2	53.4	31.9	17.5	8.92	3.31	1.77	1.55
09	1.95	5.00	8.57	16.4	11.8	48.1	33.2	16.6	10.1	3.21	1.62	1.55
10	1.95	4.50	8.07	16.4	18.5	41.5	32.2	15.7	10.1	3.10	1.55	1.55
11	1.95	4.25	7.74	16.4	74.8	42.2	31.6	15.5	9.61	3.10	1.55	1.55
12	2.31	4.02	7.57	16.4	36.0	73.2	32.5	16.0	9.61	3.10	1.55	1.55
13	2.41	3.79	7.24	16.4	25.2	63.3	40.9	17.3	9.61	3.21	1.55	1.55
14	2.21	3.91	7.08	16.4	21.6	55.4	39.9	16.2	10.3	3.10	1.55	1.55
15	2.11	4.63	6.91	17.1	19.7	48.9	36.0	16.6	9.77	3.10	1.55	1.55
16	2.11	5.78	7.74	18.2	17.5	43.5	33.5	19.2	9.77	3.10	1.55	1.55
17	2.31	4.75	9.61	17.8	16.8	39.6	31.9	17.5	8.92	2.76	1.55	1.55
18	2.80	8.57	19.7	17.8	27.1	36.4	31.6	16.8	8.92	2.45	1.55	1.55
19	3.10	9.61	21.0	24.9	43.8	36.0	30.3	16.4	8.92	2.45	1.55	1.69
20	3.10	17.8	20.3	33.5	53.8	32.5	31.6	17.0	8.74	2.45	1.55	2.11
21	3.10	20.5	19.7	24.0	49.3	30.3	31.2	19.2	7.69	2.45	1.55	2.53
22	3.10	20.5	18.7	22.2	46.2	29.6	29.3	20.2	7.22	2.45	1.55	2.99
23	2.90	20.5	18.5	22.2	43.5	32.8	27.4	19.9	6.60	2.45	1.55	3.42
24	2.90	20.5	18.2	21.3	43.5	39.6	26.5	19.0	6.29	2.36	1.55	3.21
25	2.90	21.9	18.0	21.0	55.4	41.2	25.5	18.2	5.75	2.36	1.55	3.10
26	3.00	28.7	17.8	20.8	81.6	36.4	23.2	18.7	5.50	2.11	1.55	3.21
27	3.10	27.1	17.8	20.0	69.4	34.1	21.6	18.0	5.24	1.77	1.55	3.21
28	3.00	23.1	17.6	19.2	59.5	32.8	20.9	16.4	5.88	1.77	1.55	3.21
29	2.90	20.5	17.6	18.0	-----	32.5	20.9	14.7	6.44	1.86	1.55	3.31
30	2.90	20.5	17.6	18.0	-----	35.1	20.6	13.0	6.13	1.77	1.55	3.42
31	3.56	-----	17.3	18.5	-----	35.7	-----	13.2	-----	1.77	1.55	-----
Maks.	4.25	36.0	21.9	48.1	104.	200.	42.8	21.6	13.0	5.62	1.77	3.88
Min.	1.72	3.10	6.91	15.9	11.5	28.4	19.9	12.4	5.11	1.77	1.55	1.55
Ortalama	2.57	11.2	13.1	19.2	33.9	48.8	30.1	17.5	8.82	2.98	1.61	2.11
LT/SN/Km2	2.19	9.53	11.1	16.3	28.9	41.5	25.6	14.9	7.51	2.54	1.37	1.80
AKIM mm.	5.85	24.7	29.9	43.8	69.9	111.	66.5	39.9	19.5	6.81	3.67	4.66
MİL. M3	6.87	29.0	35.1	51.4	82.1	131.	78.0	46.9	22.9	7.99	4.31	5.47

SU YILI (2006) YILLIK TOPLAM AKIM 501.04 MİLYON M3 427 MM. 13.5 LT/SN/Km2

12. Sakarya Havzasi

D12A155 AKÇASU ORTAKÖY

YERİ : **BURSA-İNEGÖL KAZASINDAN ANKARA İSTİKAMETİNE DEVAM EDİLEREKALİBEY KÖYÜ YOLUNA DÖNÜLÜR**
29°34'0" Doğu - 40°1'0" Kuzey

YAĞIŞ ALANI : **106,32 km2** **YAKLAŞIK KOT : 318 m**

GÖZLEM SÜRESİ : **21.08.1981 - 30.09.2006**

ORTALAMA AKIMLAR : **Gözlem süresinde 1.631 m3/sn. (22 Yıllık) 2006 Su yılında 1.697 m3/sn.**

ANLIK EN ÇOK VE EN AZ AKIMLAR:

2006 Su yılında anlık ençok akım	**:**	**23.1**	**m3/sn**	**03.03.2006**
2006 Su yılında anlık enaz akım	**:**	**0.001**	**m3/sn**	**22.08.2006**
Gözlem süresinde anlık ençok akım	**:**	**72.0**	**m3/sn**	**25.12.2001**
Gözlem süresinde anlık enaz akım	**:**	**0.000**	**m3/sn**	**22.09.1984**

İstasyon için kullanılmış anahtar bulunamadı.

Akımlar 01 Ekim 2005 'den 30 Eylül 2006' a kadar m3/sn olarak

Gün	Ekim	Kasım	Aralık	Ocak	Şubat	Mart	Nisan	Mayıs	Haziran	Temmuz	Ağustos	Eylül
01	0.082	0.355	1.55	4.10	1.40	7.83	4.50	2.02	0.760	0.290	0.082	0.040
02	0.082	0.355	1.40	2.90	1.40	7.30	4.30	1.86	0.760	0.210	0.082	0.082
03	0.140	0.355	1.40	2.34	1.40	14.4	4.10	1.86	0.670	0.210	0.040	0.040
04	0.082	0.355	1.27	2.18	1.27	10.7	4.10	1.70	0.670	0.290	0.082	0.010
05	0.082	0.420	1.27	1.86	1.27	8.10	3.90	1.70	0.580	0.210	0.082	0.010
06	0.082	0.670	1.13	1.86	1.70	7.03	3.90	1.55	0.580	0.210	0.082	0.010
07	0.082	0.760	1.00	1.86	1.70	6.77	3.90	1.70	0.580	0.210	0.082	0.010
08	0.082	0.580	1.00	2.02	1.55	7.57	4.10	1.55	0.580	0.210	0.082	0.005
09	0.082	0.500	1.00	1.86	1.40	6.50	4.10	1.55	0.580	0.210	0.010	0.010
10	0.082	0.420	0.880	1.70	2.02	5.83	3.90	1.55	0.580	0.210	0.010	0.040
11	0.082	0.420	0.880	1.55	6.05	5.83	3.70	1.55	0.500	0.210	0.010	0.010
12	0.210	0.420	0.880	1.40	3.70	9.55	3.90	1.55	0.580	0.210	0.040	0.040
13	0.140	0.420	0.760	1.40	2.90	8.97	4.30	1.70	0.500	0.210	0.040	0.010
14	0.140	0.420	0.670	1.40	2.50	7.83	4.10	1.55	0.580	0.210	0.040	0.010
15	0.082	0.670	0.670	1.40	2.18	6.77	3.90	1.70	0.500	0.210	0.010	0.040
16	0.082	0.670	0.760	1.40	2.02	6.28	3.50	1.70	0.500	0.210	0.010	0.082
17	0.140	0.500	0.880	1.27	2.02	5.60	3.30	1.55	0.500	0.210	0.005	0.010
18	0.290	1.70	1.00	1.27	3.50	5.38	3.30	1.55	0.500	0.210	0.010	0.010
19	0.290	1.40	2.34	1.86	4.93	5.15	3.10	1.40	0.420	0.210	0.010	0.210
20	0.290	3.10	1.70	2.18	6.05	4.50	3.30	1.40	0.420	0.210	0.005	0.290
21	0.290	2.02	1.55	1.70	5.60	4.30	3.10	1.27	0.355	0.140	0.010	0.290
22	0.290	1.27	1.55	1.55	5.38	4.30	2.90	1.27	0.290	0.210	0.001	0.290
23	0.290	1.13	1.40	1.55	5.38	4.93	2.70	1.27	0.290	0.140	0.001	0.210
24	0.290	1.40	1.13	1.40	5.60	5.83	2.50	1.27	0.290	0.140	0.010	0.210
25	0.290	3.70	1.00	1.40	7.30	5.83	2.50	1.27	0.290	0.140	0.001	0.210
26	0.290	4.50	1.00	1.40	9.26	5.15	2.18	1.13	0.210	0.082	0.010	0.210
27	0.290	3.50	1.13	1.40	8.68	4.93	2.02	1.00	0.210	0.082	0.001	0.140
28	0.290	2.90	1.86	1.40	7.57	4.50	1.86	1.00	0.290	0.082	0.010	0.355
29	0.290	2.18	2.90	1.27	-----	4.50	1.86	0.880	0.355	0.082	0.010	0.670
30	0.355	1.86	2.50	1.40	-----	4.93	2.02	0.880	0.290	0.040	0.010	0.500
31	0.420	-----	4.50	1.40	-----	4.93	-----	0.760	-----	0.040	0.005	-----
Maks.	0.500	5.83	6.50	5.38	11.9	23.1	4.93	3.10	0.880	0.420	0.210	0.670
Min.	0.082	0.355	0.670	1.13	1.13	4.30	1.86	0.670	0.140	0.040	0.001	0.005
Ortalama	0.194	1.30	1.39	1.73	3.78	6.52	3.36	1.44	0.474	0.179	0.028	0.135
LT/SN/Km2	1.82	12.2	13.0	16.3	35.5	61.3	31.6	13.6	4.46	1.68	0.268	1.27
AKIM mm.	4.88	31.7	34.9	43.6	85.9	164.	81.9	36.3	11.5	4.50	0.718	3.29
MİL. M3	0.519	3.37	3.71	4.64	9.14	17.5	8.71	3.86	1.23	0.478	0.076	0.350

SU YILI (2006) YILLIK TOPLAM AKIM 53.58 MİLYON M3 504 MM. 16.0 LT/SN/Km2

12. Sakarya Havzasi

D12A159 GÖKPİNAR D. AYDİNLI

YERİ : **ESKİŞEHİR ANKARA YOLU 100.KM.DEN SOLA AYRILAN 60.KM.DEKİAYDINLI KÖYÜNE 4.KM MESAFEDEDİR**
LİMNIGRAFLI
31°45'0" Doğu - 39°6'0" Kuzey

YAĞIŞ ALANI : **2117.20 km2** **YAKLAŞIK KOT : 790 m**

GÖZLEM SÜRESİ : **01.07.1981 - 30.09.2006**

ORTALAMA AKIMLAR : **Gözlem süresinde 5.264 m3/sn. (27 Yıllık) 2006 Su yılında 3.063 m3/sn.**

ANLIK EN ÇOK VE EN AZ AKIMLAR:

2006 Su yılında anlık ençok akım	**:**	**5.38**	**m3/sn**	**28.09.2006**
2006 Su yılında anlık enaz akım	**:**	**1.48**	**m3/sn**	**01.10.2005**
Gözlem süresinde anlık ençok akım	**:**	**21.0**	**m3/sn**	**06.06.1983**
Gözlem süresinde anlık enaz akım	**:**	**1.46**	**m3/sn**	**27.06.2005**

5. Anahtar Eğrisi (Seviyeler cm olarak)

Seviye	Akım	Seviye	Akım
70	0.641	109	7.0
75	0.886	119	9.6
80	1.2	130	12.3
90	2.8		
100	4.9		

Akımlar 01 Ekim 2005 'den 30 Eylül 2006' a kadar m3/sn olarak

Gün	Ekim	Kasım	Aralık	Ocak	Şubat	Mart	Nisan	Mayıs	Haziran	Temmuz	Ağustos	Eylül
01	1.48	2.47	3.01	2.47	2.31	4.50	3.65	3.01	3.01	3.87	2.80	2.64
02	1.48	2.47	3.01	2.47	2.47	4.29	3.65	3.01	3.01	3.87	2.80	3.01
03	1.48	2.64	3.01	2.47	2.47	4.29	3.65	3.01	3.01	3.87	2.64	3.01
04	1.48	2.64	3.01	2.31	2.64	4.29	3.23	3.01	3.01	3.65	2.80	3.01
05	1.48	2.80	3.01	2.31	2.80	4.08	3.44	3.23	3.01	3.44	2.64	3.01
06	1.81	2.80	3.01	2.47	3.01	4.08	3.23	3.23	3.23	3.44	2.64	2.80
07	1.81	2.80	2.80	2.47	3.01	4.29	3.23	3.23	3.23	3.44	2.47	2.80
08	1.81	2.80	2.80	2.31	3.23	4.08	3.23	3.23	3.23	3.23	2.47	2.80
09	1.98	2.64	2.80	2.31	2.80	4.29	3.01	3.23	3.23	3.23	2.47	2.80
10	1.98	2.64	3.01	2.31	2.64	4.08	3.01	3.23	3.23	3.01	2.31	2.80
11	1.98	2.64	2.80	2.31	3.23	4.08	3.23	3.23	3.44	3.01	2.31	3.01
12	1.98	2.80	2.80	2.31	3.65	4.08	3.23	3.23	3.44	3.23	2.14	4.08
13	2.31	2.80	2.64	2.31	3.44	3.87	3.01	3.44	3.44	3.01	2.14	4.08
14	2.47	2.80	2.80	2.31	3.44	4.08	3.01	3.44	3.65	3.01	2.14	4.08
15	2.14	3.01	2.80	2.31	3.23	4.08	3.01	3.23	3.87	3.23	2.14	4.08
16	2.14	3.01	2.64	2.31	3.23	4.08	3.01	3.23	3.87	3.23	2.14	4.08
17	2.14	3.01	2.47	2.31	3.23	3.87	3.01	3.44	3.44	3.23	2.14	4.08
18	2.31	2.80	2.47	2.47	3.44	3.87	3.01	3.44	3.44	3.23	2.47	4.08
19	2.31	2.80	2.47	2.47	3.65	3.87	3.01	3.44	3.23	3.23	2.64	4.08
20	2.31	3.23	2.64	2.64	3.65	4.08	3.01	3.44	3.23	3.23	2.47	4.29
21	2.31	3.01	2.64	2.64	3.87	4.08	3.01	3.44	3.23	3.23	2.47	4.50
22	2.31	3.23	2.31	2.64	3.87	4.08	3.01	3.44	3.01	3.01	2.47	4.50
23	2.14	3.23	2.47	2.64	3.65	3.87	2.80	3.44	3.01	3.01	2.47	4.50
24	2.14	3.23	2.47	2.64	4.08	4.29	3.01	3.23	3.44	3.01	2.31	4.50
25	2.14	3.23	2.47	2.47	4.50	4.50	2.80	3.23	3.65	3.01	2.31	4.50
26	2.47	3.01	2.47	2.64	4.50	4.50	2.80	3.23	3.65	2.80	2.14	4.72
27	2.47	3.23	2.47	2.64	4.50	4.29	2.80	3.23	3.65	2.80	2.14	4.72
28	2.47	3.01	2.31	2.47	4.50	4.29	2.80	3.23	3.65	2.80	2.14	5.15
29	2.47	3.01	2.47	2.47	-----	4.08	2.80	3.23	3.87	2.80	2.47	5.15
30	2.64	3.01	2.47	2.47	-----	3.87	2.80	3.23	3.87	2.80	2.64	5.15
31	2.64	-----	2.47	2.31	-----	3.87	-----	3.01	-----	2.80	2.47	-----
Maks.	2.64	3.44	3.01	2.80	4.72	4.93	3.87	3.44	4.08	4.08	3.01	5.38
Min.	1.48	2.47	2.31	2.31	2.31	3.87	2.64	3.01	3.01	2.80	2.14	2.47
Ortalama	2.10	2.89	2.68	2.44	3.39	4.13	3.08	3.26	3.38	3.19	2.41	3.87
LT/SN/Km2	0.992	1.37	1.26	1.15	1.60	1.95	1.46	1.54	1.59	1.50	1.14	1.83
AKIM mm.	2.66	3.54	3.39	3.09	3.88	5.22	3.77	4.12	4.13	4.03	3.05	4.73
MİL. M3	5.62	7.50	7.17	6.54	8.21	11.1	7.99	8.72	8.75	8.53	6.46	10.0

SU YILI (2006) YILLIK TOPLAM AKIM 96.59 MİLYON M3 46 MM. 1.4 LT/SN/Km2

12. Sakarya Havzasi

D12A160 SÖĞÜT D. KÜRE

YERİ : **SÖĞÜT BİLECİK ASFALTININ 10.KM DEN SOLA AYRILAN TOPRAKYOLUN 4.CÜ KM DEDİR.LİMNIGRAFLI**

30°7'0" Doğu - 40°3'0" Kuzey

YAĞIŞ ALANI : **94.19 km2** **YAKLAŞIK KOT : 510 m**

GÖZLEM SÜRESİ : **26.01.1981 - 30.09.2006**

ORTALAMA AKIMLAR : **Gözlem süresinde 0.347 m3/sn. (10 Yıllık) 2006 Su yılında 0.347 m3/sn.**

ANLIK EN ÇOK VE EN AZ AKIMLAR:

2006 Su yılında anlık ençok akım	**:**	**1.60**	**m3/sn**	**20.03.2006**
2006 Su yılında anlık enaz akım	**:**	**0.000**	**m3/sn**	**05.12.2005**
Gözlem süresinde anlık ençok akım	**:**	**17.0**	**m3/sn**	**11.06.1986**
Gözlem süresinde anlık enaz akım	**:**	**0.000**	**m3/sn**	**05.12.2005**

Akımlar 01 Ekim 2005 'den 30 Eylül 2006' a kadar m3/sn olarak

Gün	Ekim	Kasım	Aralık	Ocak	Şubat	Mart	Nisan	Mayıs	Haziran	Temmuz	Ağustos	Eylül
01	0.211	0.141	0.001	0.015	0.070	1.40	0.430	0.350	0.269	0.062	0.350	0.228
02	0.211	0.141	0.001	0.015	0.270	1.40	0.430	0.350	0.269	0.269	0.350	0.228
03	0.211	0.141	0.001	0.015	0.270	1.40	0.430	0.350	0.269	0.310	0.350	0.228
04	0.211	0.141	0.001	0.015	0.500	1.40	0.430	0.350	0.269	0.228	0.350	0.228
05	0.211	0.141	0.170	0.015	0.880	1.40	0.430	0.350	0.269	0.228	0.350	0.228
06	0.211	0.141	0.170	0.015	0.880	1.40	0.430	0.350	0.269	0.228	0.350	0.228
07	0.211	0.141	0.029	0.015	0.880	1.40	0.430	0.350	0.269	0.228	0.350	0.228
08	0.211	0.141	0.029	0.015	1.05	1.40	0.430	0.350	0.269	0.310	0.350	0.187
09	0.211	0.141	0.029	0.015	1.30	1.40	0.430	0.350	0.269	0.310	0.350	0.158
10	0.357	0.141	0.029	0.015	1.30	1.40	0.430	0.350	0.269	0.310	0.350	0.158
11	0.211	0.037	0.015	0.015	1.30	1.40	0.430	0.350	0.269	0.310	0.350	0.158
12	0.176	0.003	0.015	0.015	1.40	1.40	0.430	0.350	0.269	0.310	0.350	0.158
13	0.176	0.003	0.015	0.015	1.40	1.40	0.430	0.350	0.269	0.350	0.350	0.158
14	0.176	0.003	0.015	0.015	1.40	1.40	0.430	0.350	0.310	0.350	0.350	0.128
15	0.176	0.003	0.015	0.015	1.40	1.40	0.430	0.310	0.310	0.350	0.350	0.158
16	0.141	0.003	0.015	0.015	1.40	1.40	0.430	0.269	0.310	0.187	0.350	0.158
17	0.141	0.003	0.015	0.015	1.40	1.40	0.228	0.269	0.310	0.062	0.350	0.158
18	0.141	0.003	0.015	0.015	1.40	1.40	0.350	0.269	0.310	0.062	0.350	0.158
19	0.141	0.001	0.015	0.015	1.40	1.40	0.350	0.269	0.310	0.104	0.350	0.158
20	0.141	0.001	0.015	0.015	1.40	0.980	0.350	0.269	0.269	0.228	0.350	0.158
21	0.141	0.001	0.015	0.015	1.40	0.500	0.350	0.269	0.269	0.228	0.350	0.128
22	0.141	0.001	0.015	0.015	1.40	0.500	0.350	0.269	0.269	0.228	0.350	0.158
23	0.141	0.001	0.015	0.015	1.40	0.500	0.350	0.269	0.269	0.228	0.350	0.158
24	0.141	0.001	0.015	0.015	1.40	0.500	0.350	0.269	0.269	0.228	0.350	0.158
25	0.141	0.001	0.015	0.015	1.40	0.500	0.350	0.269	0.269	0.228	0.350	0.158
26	0.141	0.001	0.015	0.015	1.40	0.500	0.350	0.269	0.269	0.228	0.350	0.187
27	0.141	0.001	0.015	0.015	1.40	0.500	0.350	0.269	0.269	0.310	0.350	0.128
28	0.141	0.001	0.015	0.015	1.40	0.500	0.350	0.269	0.269	0.350	0.269	0.260
29	0.141	0.001	0.015	0.015	-----	0.500	0.350	0.269	0.128	0.350	0.228	0.260
30	0.141	0.001	0.015	0.015	-----	0.500	0.350	0.310	0.062	0.350	0.228	0.211
31	0.141	-----	0.015	0.015	-----	0.500	-----	0.310	-----	0.350	0.228	-----
Maks.	0.591	0.211	1.20	0.047	1.40	1.60	0.430	0.545	0.310	0.685	0.754	1.14
Min.	0.141	0.001	KURU	0.015	0.015	0.500	0.228	0.269	0.062	0.062	0.228	0.062
Ortalama	0.175	0.049	0.025	0.015	1.16	1.07	0.389	0.310	0.266	0.254	0.336	0.182
LT/SN/Km2	1.86	0.524	0.265	0.159	12.3	11.3	4.13	3.29	2.82	2.70	3.56	1.93
AKIM mm.	4.98	1.36	0.711	0.427	29.8	30.3	10.7	8.80	7.31	7.22	9.54	5.00
MİL. M3	0.469	0.128	0.067	0.040	2.81	2.86	1.01	0.829	0.688	0.680	0.899	0.471

SU YILI (2006) YILLIK TOPLAM AKIM 10.95 MİLYON M3 116 MM. 3.7 LT/SN/Km2

12. Sakarya Havzasi

D12A164 BOĞAZDERE MAHMUDİYE

YERİ : **BURSA-YENİŞEHİR İLÇESİNİN İNEGÖL İLÇESİ ÇIKIŞINDAN SOLADÖNÜLEREK 8 KM SONRA MAHMUDİYE KÖYÜNE GELMEDEN ÖNCEKİ KÖP-**
29°41'15" Doğu - 40°13'45" Kuzey

YAĞIŞ ALANI : **62,60 km2** **YAKLAŞIK KOT : 256 m**

GÖZLEM SÜRESİ : **20.09.1982 - 30.09.2006**

ORTALAMA AKIMLAR : **Gözlem süresinde 0.417 m3/sn. (21 Yıllık) 2006 Su yılında 0.382 m3/sn.**

ANLIK EN ÇOK VE EN AZ AKIMLAR:

2006 Su yılında anlık ençok akım	:	**6.87**	**m3/sn**	**20.02.2006**
2006 Su yılında anlık enaz akım	:	**0.000**	**m3/sn**	**09.08.2006**
Gözlem süresinde anlık ençok akım	:	**39.0**	**m3/sn**	**11.03.2000**
Gözlem süresinde anlık enaz akım	:	**0.000**	**m3/sn**	**26.06.1983**

İstasyon için kullanılmış anahtar bulunamadı.

Akımlar 01 Ekim 2005 'den 30 Eylül 2006' a kadar m3/sn olarak

Gün	Ekim	Kasım	Aralık	Ocak	Şubat	Mart	Nisan	Mayıs	Haziran	Temmuz	Ağustos	Eylül
01	0.029	0.149	0.257	0.471	0.365	2.00	0.365	0.365	0.149	0.048	0.001	KURU
02	0.048	0.149	0.257	0.304	0.365	1.90	0.365	0.365	0.149	0.107	0.001	KURU
03	0.257	0.149	0.257	0.257	0.365	1.90	0.365	0.365	0.149	0.107	0.001	KURU
04	0.149	0.149	0.257	0.257	0.365	1.60	0.365	0.365	0.149	0.107	0.001	KURU
05	0.149	0.149	0.257	0.257	0.365	1.30	0.471	0.365	0.149	0.107	0.001	KURU
06	0.149	0.149	0.257	0.257	0.471	1.30	0.559	0.365	0.149	0.107	0.001	KURU
07	0.149	0.149	0.257	0.257	0.559	1.30	0.559	0.304	0.107	0.073	0.001	KURU
08	0.149	0.149	0.257	0.257	0.559	1.30	0.559	0.304	0.073	0.073	0.001	KURU
09	0.149	0.149	0.257	0.257	0.559	1.30	0.559	0.365	0.048	0.073	KURU	KURU
10	0.149	0.149	0.257	0.257	0.775	1.30	0.559	0.365	0.048	0.073	KURU	KURU
11	0.149	0.149	0.257	0.257	2.83	1.60	0.559	0.365	0.048	0.048	KURU	KURU
12	0.149	0.149	0.257	0.257	1.87	1.51	0.471	0.365	0.073	0.048	KURU	KURU
13	0.149	0.149	0.193	0.257	1.38	1.24	0.471	0.365	0.149	0.048	KURU	KURU
14	0.149	0.149	0.149	0.257	1.24	1.12	0.471	0.365	0.149	0.048	KURU	KURU
15	0.149	0.149	0.149	0.257	1.12	1.00	0.471	0.365	0.149	0.029	KURU	KURU
16	0.107	0.149	0.149	0.257	0.775	1.00	0.471	0.365	0.193	0.029	KURU	KURU
17	0.107	0.149	0.149	0.257	0.775	1.00	0.471	0.365	0.257	0.017	KURU	KURU
18	0.107	0.149	0.149	0.257	2.01	0.888	0.471	0.365	0.257	0.010	KURU	KURU
19	0.107	0.149	0.149	0.304	3.56	0.775	0.471	0.365	0.257	0.010	KURU	0.001
20	0.107	0.149	0.193	0.559	4.43	0.775	0.471	0.365	0.257	0.010	KURU	0.002
21	0.107	0.193	0.193	0.559	3.50	0.775	0.471	0.365	0.257	0.010	KURU	0.005
22	0.107	0.193	0.149	0.471	3.20	0.775	0.471	0.365	0.193	0.005	KURU	0.005
23	0.073	0.193	0.149	0.365	2.80	0.775	0.471	0.304	0.193	0.005	KURU	0.001
24	0.073	0.193	0.149	0.304	2.90	0.775	0.471	0.304	0.193	0.005	KURU	KURU
25	0.073	0.257	0.149	0.304	2.90	0.775	0.471	0.304	0.193	0.010	KURU	0.005
26	0.073	0.662	0.149	0.304	2.50	0.775	0.471	0.304	0.149	0.002	KURU	0.048
27	0.073	0.471	0.257	0.304	2.10	0.662	0.471	0.304	0.149	0.001	KURU	0.048
28	0.073	0.471	0.888	0.304	2.00	0.662	0.365	0.304	0.149	0.001	KURU	0.048
29	0.107	0.304	0.888	0.304	-----	0.662	0.365	0.257	0.149	0.001	KURU	0.257
30	0.107	0.257	0.662	0.365	-----	0.662	0.365	0.193	0.149	0.001	KURU	0.193
31	0.107	-----	0.471	0.365	-----	0.559	-----	0.149	-----	0.001	KURU	-----
Maks.	0.365	0.888	1.00	0.775	6.87	2.60	0.559	0.471	0.257	0.775	0.001	0.365
Min.	0.029	0.107	0.149	0.257	0.304	0.365	0.365	0.149	0.010	0.001	KURU	KURU
Ortalama	0.117	0.206	0.273	0.313	1.67	1.10	0.464	0.333	0.158	0.039	0.000	0.020
LT/SN/Km2	1.87	3.29	4.36	5.00	26.6	17.5	7.41	5.32	2.52	0.626	0.004	0.326
AKIM mm.	5.01	8.52	11.7	13.4	64.4	46.9	19.2	14.3	6.53	1.68	0.011	0.846
MİL. M3	0.314	0.533	0.732	0.838	4.03	2.93	1.20	0.893	0.409	0.105	0.001	0.053

SU YILI (2006) YILLIK TOPLAM AKIM 12.04 MİLYON M3 192 MM. 6.1 LT/SN/Km2

12. Sakarya Havzasi

D12A167 PAPAZ D. AHİLER

YERİ : ADAPAZARI-MEKECE İSTİKAMETİ 70.KM DEDİR.LİMNIGRAFLI
29°59'0" Doğu - 40°28'0" Kuzey

YAĞIŞ ALANI : 101.00 km2 **YAKLAŞIK KOT :** 163 m

GÖZLEM SÜRESİ : 01.10.1982 - 30.09.2006

ORTALAMA AKIMLAR : Gözlem süresinde 0.659 m3/sn. (20 Yıllık) 2006 Su yılında 0.507 m3/sn.

ANLIK EN ÇOK VE EN AZ AKIMLAR:

2006 Su yılında anlık ençok akım	:	11.3	m3/sn	06.07.2006
2006 Su yılında anlık enaz akım	:	0.002	m3/sn	21.10.2005
Gözlem süresinde anlık ençok akım	:	58.0	m3/sn	20.01.1987
Gözlem süresinde anlık enaz akım	:	0.000	m3/sn	30.01.1987

5. Anahtar Eğrisi (Seviyeler cm olarak)

Seviye	Akım	Seviye	Akım	Seviye	Akım	Seviye	Akım
1	0.002	12	0.286	28	2.7	60	10.8
3	0.011	16	0.769	30	3.2	70	13.5
5	0.030	20	1.3	35	4.3	80	16.6
7	0.060	24	1.9	40	5.7	90	19.9
9	0.108	26	2.3	50	8.3	100	23.4

Akımlar 01 Ekim 2005 'den 30 Eylül 2006' a kadar m3/sn olarak

Gün	Ekim	Kasım	Aralık	Ocak	Şubat	Mart	Nisan	Mayıs	Haziran	Temmuz	Ağustos	Eylül
01	0.150	0.218	0.286	2.52	0.395	3.65	0.286	0.108	0.083	0.108	0.083	0.060
02	0.150	0.218	0.286	1.33	0.395	3.23	0.218	0.108	0.083	0.108	0.083	0.060
03	0.150	0.218	0.286	0.895	0.286	3.65	0.218	0.108	0.083	0.108	0.083	0.060
04	0.150	0.218	0.286	0.769	0.286	3.65	0.218	0.108	0.108	0.108	0.083	0.060
05	0.150	0.218	0.218	0.395	0.286	2.69	0.218	0.218	0.083	0.108	0.060	0.060
06	0.150	0.218	0.218	0.286	0.286	2.13	0.503	0.150	0.108	0.083	0.060	0.060
07	0.150	0.395	0.218	0.286	0.286	2.34	0.636	0.286	0.150	0.083	0.060	0.060
08	0.150	0.218	0.218	0.286	0.286	1.91	0.286	0.286	0.150	0.083	0.060	0.060
09	0.150	0.218	0.218	0.286	0.286	1.76	0.636	0.286	0.083	0.083	0.083	0.083
10	0.150	0.218	0.218	0.286	0.286	1.60	0.218	0.286	0.083	0.083	0.083	0.083
11	0.150	0.218	0.218	0.286	5.70	1.47	0.218	0.286	0.083	0.083	0.083	0.083
12	0.150	0.286	0.218	0.286	2.96	1.18	0.218	0.286	0.108	0.083	0.083	0.083
13	0.150	0.218	0.218	0.286	1.76	1.18	0.218	0.286	0.218	0.083	0.083	0.083
14	0.150	0.218	0.218	0.286	1.18	1.18	0.218	0.150	0.395	0.083	0.083	0.043
15	0.150	0.218	0.286	0.286	0.895	1.18	0.218	0.150	0.395	0.083	0.083	0.043
16	0.150	0.218	0.395	0.286	0.769	1.02	0.218	0.218	0.395	0.060	0.083	0.043
17	0.150	0.150	1.02	0.395	0.503	1.02	0.218	0.286	0.395	0.060	0.083	0.043
18	0.150	1.18	0.769	0.286	0.503	0.895	0.150	0.286	0.286	0.060	0.083	0.030
19	0.150	0.503	1.33	0.286	1.02	0.769	0.150	0.286	0.286	0.060	0.083	0.030
20	0.108	1.47	1.18	0.286	2.34	1.18	0.150	0.286	0.286	0.060	0.043	0.030
21	0.108	1.02	0.769	0.286	2.52	0.895	0.150	0.286	0.218	0.060	0.043	0.030
22	0.218	0.636	0.636	0.286	2.52	0.769	0.150	0.286	0.218	0.060	0.043	0.030
23	0.218	0.395	0.769	0.286	3.65	0.769	0.150	0.286	0.218	0.060	0.108	0.030
24	0.218	1.47	0.769	0.286	3.44	0.895	0.150	0.218	0.218	0.060	0.030	0.030
25	0.218	4.07	0.636	0.286	3.44	0.895	0.150	0.150	0.108	0.060	0.030	0.030
26	0.218	4.28	0.395	0.286	6.48	0.769	0.150	0.150	0.108	0.060	0.060	0.043
27	0.218	2.52	0.218	0.286	5.13	0.503	0.150	0.150	0.108	0.060	0.060	0.043
28	0.218	1.91	0.503	0.286	3.86	0.395	0.150	0.150	0.108	0.060	0.060	0.043
29	0.218	1.33	2.13	0.395	-----	0.286	0.150	0.150	0.150	0.060	0.060	0.043
30	0.218	0.769	0.895	0.395	-----	0.286	0.150	0.108	0.150	0.060	0.060	0.043
31	0.218	-----	3.44	0.395	-----	0.286	-----	0.083	-----	0.083	0.060	-----
Maks.	0.769	7.00	6.22	4.07	7.52	3.65	1.18	2.34	0.395	11.3	0.108	0.083
Min.	0.002	0.019	0.218	0.150	0.286	0.286	0.150	0.011	0.083	0.060	0.030	0.011
Ortalama	0.169	0.848	0.628	0.445	1.85	1.43	0.230	0.209	0.182	0.076	0.069	0.051
LT/SN/Km2	1.68	8.39	6.22	4.40	18.3	14.2	2.28	2.07	1.80	0.752	0.684	0.502
AKIM mm.	4.49	21.8	16.7	11.8	44.3	38.0	5.91	5.54	4.68	2.01	1.83	1.30
MİL. M3	0.453	2.20	1.68	1.19	4.47	3.84	0.597	0.560	0.472	0.203	0.185	0.132

SU YILI (2006) YILLIK TOPLAM AKIM 15.98 MİLYON M3 158 MM. 5.0 LT/SN/Km2

12. Sakarya Havzasi

D12A170 SARISU KANDİLLİ

YERİ : **ESKİŞEHİR-ÇUKURHİSAR KASABASINDAN SOLA SAPAN YOLUN12 KM DEDİR.EŞELLİ**
30°2'0" Doğu - 39°49'0" Kuzey

YAĞIŞ ALANI : **215.50 km2** **YAKLAŞIK KOT : 870 m**

GÖZLEM SÜRESİ : **01.06.1983 - 30.09.2006**

ORTALAMA AKIMLAR : **Gözlem süresinde 0.316 m3/sn. (21 Yıllık) 2006 Su yılında 0.282 m3/sn.**

ANLIK EN ÇOK VE EN AZ AKIMLAR:

2006 Su yılında anlık ençok akım	**:**	**1.80**	**m3/sn**	**03.03.2006**
2006 Su yılında anlık enaz akım	**:**	**0.012**	**m3/sn**	**06.12.2005**
Gözlem süresinde anlık ençok akım	**:**	**6.00**	**m3/sn**	**23.03.1987**
Gözlem süresinde anlık enaz akım	**:**	**0.000**	**m3/sn**	**28.03.1989**

1. Anahtar Eğrisi (Seviyeler cm olarak)

Seviye	Akım	Seviye	Akım	Seviye	Akım	Seviye	Akım
1	0.001	11	0.330	19	0.910	27	1.8
3	0.031	13	0.440	20	1.0	29	2.0
5	0.084	15	0.580	21	1.1	31	2.3
7	0.150	17	0.740	23	1.3	41	4.2
9	0.230	18	0.830	25	1.5	51	6.4

Akımlar 01 Ekim 2005 'den 30 Eylül 2006' a kadar m3/sn olarak

Gün	Ekim	Kasım	Aralık	Ocak	Şubat	Mart	Nisan	Mayıs	Haziran	Temmuz	Ağustos	Eylül
01	0.380	0.031	0.031	0.012	0.012	0.510	0.115	0.580	0.740	0.830	0.230	0.830
02	0.380	0.031	0.031	0.012	0.012	0.380	0.115	0.115	0.830	0.830	0.740	0.830
03	0.330	0.031	0.031	0.012	0.031	1.10	0.115	0.115	0.830	0.910	0.830	0.740
04	0.330	0.031	0.031	0.012	0.031	0.440	0.115	0.115	0.910	1.00	0.830	0.660
05	0.280	0.031	0.031	0.012	0.031	0.230	0.115	0.115	0.910	1.00	0.910	0.660
06	0.280	0.031	0.031	0.012	0.031	0.230	0.115	0.084	0.910	0.910	0.910	0.660
07	0.230	0.031	0.031	0.012	0.031	0.150	0.115	0.115	0.910	0.830	0.910	0.660
08	0.230	0.031	0.031	0.012	0.031	0.150	0.115	0.084	0.910	0.910	0.910	0.660
09	0.190	0.031	0.031	0.012	0.031	0.150	0.115	0.084	0.910	0.910	0.910	0.660
10	0.190	0.031	0.031	0.012	0.031	0.115	0.115	0.084	0.910	0.910	0.910	0.660
11	0.150	0.031	0.031	0.012	0.031	0.115	0.115	0.084	0.830	0.830	0.910	0.580
12	0.150	0.031	0.031	0.012	0.031	0.115	0.055	0.084	0.830	0.830	0.910	0.580
13	0.115	0.031	0.031	0.012	0.031	0.115	0.055	0.084	0.830	0.910	0.830	0.580
14	0.115	0.031	0.031	0.012	0.031	0.230	0.055	0.084	0.510	0.910	0.830	0.580
15	0.084	0.031	0.031	0.012	0.031	0.230	0.031	0.084	0.115	0.910	0.830	0.580
16	0.084	0.031	0.031	0.012	0.031	0.190	0.031	0.084	0.115	0.910	0.830	0.580
17	0.055	0.031	0.031	0.012	0.031	0.190	0.031	0.084	0.115	0.910	0.830	0.580
18	0.031	0.031	0.031	0.012	0.031	0.150	0.031	0.084	0.115	0.910	0.830	0.580
19	0.031	0.031	0.031	0.012	0.031	0.150	0.031	0.084	0.115	0.910	0.830	0.580
20	0.031	0.031	0.031	0.012	0.031	0.150	0.031	0.084	0.115	0.830	0.830	0.330
21	0.031	0.031	0.031	0.012	0.031	0.150	0.031	0.055	0.115	0.830	0.830	0.055
22	0.031	0.031	0.031	0.012	0.031	0.115	0.031	0.055	0.660	0.830	0.830	0.031
23	0.031	0.031	0.031	0.012	0.031	0.115	0.055	0.055	0.830	0.830	0.830	0.031
24	0.031	0.031	0.031	0.012	0.031	0.115	0.055	0.084	0.830	0.230	0.830	0.031
25	0.031	0.031	0.055	0.012	0.150	0.115	0.084	0.084	0.830	0.115	0.830	0.031
26	0.031	0.031	0.055	0.012	0.580	0.115	0.115	0.055	0.830	0.115	0.830	0.031
27	0.031	0.031	0.055	0.012	0.580	0.115	0.280	0.055	0.830	0.115	0.830	0.031
28	0.031	0.031	0.055	0.012	0.440	0.115	0.280	0.084	0.830	0.084	0.830	0.031
29	0.031	0.031	0.055	0.012	-----	0.115	0.280	0.580	0.830	0.084	0.830	0.031
30	0.031	0.031	0.031	0.012	-----	0.115	0.280	0.660	0.830	0.084	0.830	0.055
31	0.031	-----	0.012	0.012	-----	0.115	-----	0.660	-----	0.084	0.830	-----
Maks.	0.380	0.031	0.280	0.031	0.740	1.80	0.830	0.830	1.00	1.00	1.00	0.910
Min.	0.031	0.031	0.012	0.012	0.012	0.115	0.031	0.055	0.115	0.084	0.084	0.031
Ortalama	0.129	0.031	0.034	0.012	0.088	0.206	0.104	0.153	0.662	0.687	0.828	0.431
LT/SN/Km2	0.600	0.144	0.159	0.056	0.407	0.957	0.481	0.712	3.07	3.19	3.84	2.00
AKIM mm.	1.61	0.373	0.426	0.149	0.985	2.56	1.25	1.91	7.97	8.54	10.3	5.18
MİL. M3	0.346	0.080	0.092	0.032	0.212	0.552	0.268	0.411	1.72	1.84	2.22	1.12

SU YILI (2006) YILLIK TOPLAM AKIM 8.89 MİLYON M3 41 MM. 1.3 LT/SN/Km2

12. Sakarya Havzasi

D12A171 SARİSU YENİDODURGA

YERİ : **ESKİŞEHİR BOZUYÜK KAZASINDAN SOLA DÖNÜLEN ASFALT YOLUN25 KM DEKİ DODURGA KÖYÜNDEDİR**
29°55'0" Doğu - 39°46'0" Kuzey

YAĞIŞ ALANI : **121.00 km2** **YAKLAŞIK KOT : 1070 m**

GÖZLEM SÜRESİ : **01.10.1983 - 30.09.2006**

ORTALAMA AKIMLAR : **Gözlem süresinde 0.252 m3/sn. (17 Yıllık) 2006 Su yılında 0.170 m3/sn.**

ANLIK EN ÇOK VE EN AZ AKIMLAR:

2006 Su yılında anlık ençok akım	**:**	**14.0**	**m3/sn**	**03.03.2006**
2006 Su yılında anlık enaz akım	**:**	**0.000**	**m3/sn**	**17.10.2005**
Gözlem süresinde anlık ençok akım	**:**	**81.8**	**m3/sn**	**13.12.1990**
Gözlem süresinde anlık enaz akım	**:**	**0.000**	**m3/sn**	**15.05.1992**

Akımlar 01 Ekim 2005 'den 30 Eylül 2006' a kadar m3/sn olarak

Gün	Ekim	Kasım	Aralık	Ocak	Şubat	Mart	Nisan	Mayıs	Haziran	Temmuz	Ağustos	Eylül
01	0.035	0.051	0.076	0.100	0.100	2.03	0.220	0.140	0.076	0.051	0.021	0.021
02	0.035	0.051	0.051	0.100	0.100	1.63	0.180	0.100	0.076	0.051	0.021	0.021
03	0.035	0.051	0.051	0.100	0.100	5.50	0.180	0.100	0.076	0.051	0.021	0.021
04	0.035	0.076	0.051	0.100	0.100	2.36	0.180	0.100	0.076	0.051	0.021	0.021
05	0.035	0.076	0.051	0.100	0.100	1.40	0.180	0.100	0.076	0.051	0.021	0.021
06	0.035	0.076	0.051	0.100	0.100	0.890	0.180	0.100	0.076	0.051	0.021	0.021
07	0.035	0.076	0.051	0.100	0.100	0.800	0.180	0.140	0.076	0.051	0.021	0.021
08	0.035	0.076	0.051	0.100	0.100	0.975	0.180	0.140	0.076	0.051	0.021	0.021
09	0.035	0.076	0.051	0.100	0.100	0.800	0.180	0.140	0.076	0.051	0.021	0.021
10	0.035	0.076	0.051	0.100	0.100	0.600	0.180	0.140	0.076	0.051	0.021	0.021
11	0.035	0.076	0.051	0.100	0.395	0.537	0.180	0.100	0.076	0.051	0.021	0.021
12	0.035	0.076	0.051	0.100	0.395	0.537	0.140	0.100	0.076	0.051	0.021	0.021
13	0.035	0.076	0.051	0.100	0.335	0.537	0.140	0.100	0.076	0.051	0.021	0.021
14	0.035	0.076	0.051	0.100	0.335	0.710	0.140	0.100	0.051	0.051	0.021	0.021
15	0.035	0.076	0.051	0.100	0.275	0.600	0.140	0.100	0.051	0.051	0.021	0.021
16	0.035	0.076	0.051	0.076	0.275	0.537	0.140	0.100	0.051	0.035	0.021	0.021
17	0.035	0.051	0.051	0.076	0.275	0.473	0.140	0.100	0.076	0.035	0.021	0.021
18	0.051	0.051	0.051	0.076	0.229	0.473	0.140	0.100	0.051	0.035	0.021	0.021
19	0.051	0.051	0.051	0.076	0.395	0.473	0.140	0.100	0.051	0.035	0.021	0.021
20	0.051	0.076	0.051	0.100	0.454	0.473	0.100	0.100	0.051	0.035	0.021	0.021
21	0.051	0.076	0.051	0.100	0.577	0.410	0.100	0.100	0.051	0.035	0.021	0.035
22	0.051	0.051	0.051	0.100	1.02	0.410	0.100	0.076	0.051	0.035	0.021	0.035
23	0.051	0.051	0.051	0.100	1.22	0.347	0.100	0.076	0.035	0.035	0.021	0.035
24	0.051	0.051	0.051	0.100	1.11	0.347	0.100	0.076	0.051	0.035	0.021	0.035
25	0.051	0.076	0.051	0.100	1.63	0.347	0.100	0.076	0.051	0.021	0.021	0.035
26	0.051	0.076	0.051	0.100	2.47	0.347	0.076	0.076	0.051	0.021	0.021	0.035
27	0.051	0.076	0.051	0.100	2.14	0.347	0.076	0.076	0.051	0.035	0.021	0.035
28	0.051	0.076	0.051	0.100	1.63	0.347	0.100	0.076	0.051	0.035	0.021	0.035
29	0.051	0.076	0.051	0.100	-----	0.347	0.100	0.076	0.051	0.021	0.021	0.035
30	0.051	0.076	0.076	0.100	-----	0.347	0.100	0.076	0.051	0.021	0.021	0.035
31	0.051	-----	0.100	0.100	-----	0.220	-----	0.076	-----	0.021	0.021	-----
Maks.	0.076	0.100	0.180	0.180	4.36	14.0	0.220	0.180	0.180	0.051	0.035	0.051
Min.	KURU	0.051	0.051	0.076	0.076	0.220	0.076	0.076	0.035	0.021	0.021	0.021
Ortalama	0.042	0.068	0.054	0.097	0.577	0.844	0.140	0.099	0.062	0.040	0.021	0.026
LT/SN/Km2	0.349	0.566	0.448	0.801	4.77	6.97	1.15	0.816	0.513	0.335	0.174	0.212
AKIM mm.	0.935	1.47	1.20	2.15	11.5	18.7	2.99	2.18	1.33	0.896	0.465	0.550
MİL. M3	0.113	0.178	0.145	0.260	1.40	2.26	0.362	0.264	0.161	0.108	0.056	0.067

SU YILI (2006) YILLIK TOPLAM AKIM 5.37 MİLYON M3 44 MM. 1.4 LT/SN/Km2

12. Sakarya Havzasi

D12A172 SARISU İNONÜ

YERİ : **ESKİŞEHİR ÇUKURHİSAR KASABASINDAN SOLA SAPAN YOLUN 12 KM**
30°8'0" Doğu - 39°49'0" Kuzey

YAĞIŞ ALANI : **298.50 km2** **YAKLAŞIK KOT : 835 m**

GÖZLEM SÜRESİ : **01.06.1983 - 30.09.2006**

ORTALAMA AKIMLAR : **Gözlem süresinde 0.509 m3/sn. (19 Yıllık) 2006 Su yılında 0.439 m3/sn.**

ANLIK EN ÇOK VE EN AZ AKIMLAR:

2006 Su yılında anlık ençok akım	**:**	**8.56**	**m3/sn**	**25.02.2006**
2006 Su yılında anlık enaz akım	**:**	**0.218**	**m3/sn**	**17.10.2005**
Gözlem süresinde anlık ençok akım	**:**	**18.5**	**m3/sn**	**24.03.1987**
Gözlem süresinde anlık enaz akım	**:**	**0.000**	**m3/sn**	**04.11.1989**

Akımlar 01 Ekim 2005 'den 30 Eylül 2006' a kadar m3/sn olarak

Gün	Ekim	Kasım	Aralık	Ocak	Şubat	Mart	Nisan	Mayıs	Haziran	Temmuz	Ağustos	Eylül
01	0.340	0.268	0.322	0.340	0.360	1.04	0.340	0.607	0.492	0.466	0.340	0.466
02	0.340	0.286	0.304	0.340	0.360	0.866	0.340	0.570	0.420	0.420	0.400	0.544
03	0.340	0.286	0.322	0.322	0.360	1.90	0.340	0.466	0.466	0.492	0.466	0.518
04	0.340	0.286	0.322	0.322	0.360	0.940	0.340	0.466	0.440	0.570	0.340	0.544
05	0.340	0.286	0.322	0.340	0.360	0.570	0.340	0.466	0.466	0.570	0.420	0.518
06	0.340	0.286	0.304	0.340	0.360	0.440	0.340	0.466	0.466	0.644	0.440	0.544
07	0.340	0.286	0.322	0.340	0.360	0.420	0.340	0.466	0.518	0.466	0.440	0.644
08	0.340	0.286	0.304	0.340	0.360	0.440	0.340	0.466	0.607	0.466	0.440	0.440
09	0.340	0.268	0.322	0.340	0.360	0.466	0.340	0.466	0.466	0.440	0.420	0.466
10	0.322	0.322	0.322	0.340	0.380	0.440	0.340	0.440	0.544	0.466	0.492	0.492
11	0.322	0.360	0.322	0.340	0.492	0.518	0.360	0.440	0.518	0.492	0.340	0.644
12	0.322	0.340	0.322	0.340	0.420	0.466	0.360	0.420	0.518	0.492	0.400	0.644
13	0.322	0.340	0.304	0.340	0.420	0.440	0.380	0.380	0.544	0.607	0.420	0.607
14	0.322	0.340	0.304	0.340	0.420	0.544	0.380	0.420	0.755	0.492	0.420	0.607
15	0.322	0.322	0.304	0.340	0.420	0.492	0.380	0.518	0.570	0.544	0.466	0.607
16	0.304	0.322	0.304	0.340	0.400	0.440	0.380	0.466	0.380	0.544	0.518	0.607
17	0.304	0.322	0.322	0.322	0.400	0.440	0.380	0.466	0.420	0.518	0.380	0.607
18	0.286	0.322	0.304	0.322	0.440	0.420	0.360	0.420	0.420	0.544	0.440	0.607
19	0.322	0.322	0.304	0.380	0.492	0.440	0.360	0.400	0.420	0.518	0.420	0.718
20	0.250	0.322	0.322	0.380	0.570	0.420	0.360	0.440	0.420	0.607	0.440	1.10
21	0.268	0.322	0.322	0.360	0.607	0.380	0.380	0.440	0.400	0.420	0.420	0.644
22	0.268	0.322	0.322	0.360	0.718	0.360	0.380	0.440	0.492	0.492	0.466	0.466
23	0.268	0.304	0.322	0.360	0.755	0.340	0.360	0.440	0.400	0.518	0.492	0.440
24	0.268	0.304	0.322	0.360	0.792	0.340	0.380	0.440	0.466	0.492	0.544	0.440
25	0.250	0.322	0.322	0.360	1.90	0.340	0.440	0.492	0.466	0.420	0.400	0.440
26	0.268	0.322	0.322	0.360	3.30	0.340	0.420	0.360	0.466	0.400	0.440	0.420
27	0.268	0.322	0.322	0.360	2.22	0.360	0.492	0.420	0.466	0.440	0.466	0.420
28	0.268	0.304	0.322	0.360	1.38	0.360	0.492	0.420	0.492	0.322	0.492	0.400
29	0.268	0.304	0.340	0.360	-----	0.340	0.544	0.440	0.570	0.360	0.492	0.400
30	0.268	0.304	0.322	0.360	-----	0.420	0.544	0.518	0.440	0.360	0.492	0.400
31	0.286	-----	0.340	0.360	-----	0.360	-----	0.440	-----	0.340	0.570	-----
Maks.	0.380	0.440	0.400	0.518	8.56	4.40	0.570	1.74	1.90	2.06	1.82	2.22
Min.	0.218	0.234	0.286	0.322	0.360	0.234	0.340	0.340	0.380	0.304	0.322	0.400
Ortalama	0.303	0.310	0.318	0.347	0.706	0.519	0.384	0.455	0.484	0.481	0.442	0.546
LT/SN/Km2	1.02	1.04	1.07	1.16	2.36	1.74	1.29	1.52	1.62	1.61	1.48	1.83
AKIM mm.	2.72	2.69	2.85	3.12	5.72	4.65	3.34	4.08	4.20	4.32	3.97	4.75
MİL. M3	0.813	0.804	0.852	0.930	1.71	1.39	0.996	1.22	1.25	1.29	1.19	1.42

SU YILI (2006) YILLIK TOPLAM AKIM 13.86 MİLYON M3 46 MM. 1.5 LT/SN/Km2

12. Sakarya Havzasi

D12A175 KOCADERE AKİNCILAR

YERİ : **BURSA-İNEGÖL YOLUNUN 35.KM SİNDEKİ AKINCILAR KÖYÜNE GELMEDENÖNCEKİ KÖPRÜNÜN 25 M. MENBAINDADIR. (LİM) 29°25'3" Doğu - 40°7'8" Kuzey**

YAĞIŞ ALANI : **59,40 km2** **YAKLAŞIK KOT : 328 m**

GÖZLEM SÜRESİ : **25.04.1984 - 30.09.2006**

ORTALAMA AKIMLAR : **Gözlem süresinde 0.680 m3/sn. (20 Yıllık) 2006 Su yılında 0.710 m3/sn.**

ANLIK EN ÇOK VE EN AZ AKIMLAR:

2006 Su yılında anlık ençok akım	:	**6.20**	**m3/sn**	**10.02.2006**
2006 Su yılında anlık enaz akım	:	**0.003**	**m3/sn**	**14.08.2006**
Gözlem süresinde anlık ençok akım	:	**48.0**	**m3/sn**	**18.02.1992**
Gözlem süresinde anlık enaz akım	:	**0.000**	**m3/sn**	**05.07.1984**

İstasyon için kullanılmış anahtar bulunamadı.

Akımlar 01 Ekim 2005 'den 30 Eylül 2006' a kadar m3/sn olarak

Gün	Ekim	Kasım	Aralık	Ocak	Şubat	Mart	Nisan	Mayıs	Haziran	Temmuz	Ağustos	Eylül
01	0.270	0.210	0.757	1.00	0.653	2.00	0.860	1.32	0.653	0.653	0.023	0.035
02	0.270	0.210	0.757	0.860	0.653	1.80	0.757	1.32	0.757	0.653	0.023	0.035
03	0.330	0.210	0.860	0.757	0.653	2.65	0.757	1.16	0.757	0.653	0.023	0.035
04	0.330	0.210	0.860	0.757	0.653	2.20	0.757	1.16	0.757	0.653	0.023	0.035
05	0.330	0.210	0.757	0.653	0.653	2.00	0.757	1.16	0.653	0.653	0.023	0.035
06	0.330	0.210	0.757	0.653	0.860	1.80	0.757	1.32	0.653	0.653	0.023	0.035
07	0.330	0.210	0.757	0.757	0.757	1.64	0.757	1.32	0.653	0.653	0.035	0.035
08	0.330	0.210	0.653	0.860	0.757	1.80	0.757	1.16	0.757	0.653	0.023	0.035
09	0.330	0.160	0.653	0.860	0.757	1.80	0.860	1.00	0.860	0.653	0.023	0.035
10	0.390	0.160	0.653	0.757	1.64	1.64	0.860	0.860	0.860	0.653	0.023	0.035
11	0.330	0.160	0.550	0.757	3.70	1.64	1.00	0.860	0.860	0.550	0.023	0.035
12	0.330	0.160	0.550	0.653	2.00	2.20	1.32	1.00	0.860	0.210	0.014	0.035
13	0.330	0.160	0.550	0.757	1.48	1.80	1.80	1.16	0.860	0.052	0.007	0.035
14	0.270	0.160	0.550	0.757	1.32	1.80	2.00	1.16	0.860	0.072	0.007	0.035
15	0.330	0.160	0.470	0.653	1.32	1.64	2.00	1.16	0.860	0.072	0.007	0.035
16	0.330	0.160	0.550	0.653	1.16	1.64	2.00	1.32	0.860	0.052	0.007	0.035
17	0.160	0.210	0.550	0.653	1.00	1.64	1.80	1.32	0.757	0.052	0.007	0.035
18	0.129	0.210	0.550	0.653	1.80	1.64	1.64	1.16	0.757	0.052	0.007	0.035
19	0.129	0.210	1.00	1.32	2.20	1.48	1.64	1.00	0.653	0.035	0.014	0.052
20	0.160	0.390	0.757	1.48	2.65	1.32	1.64	0.860	0.653	0.035	0.014	0.098
21	0.160	0.390	0.653	1.00	2.20	1.16	1.64	0.860	0.653	0.035	0.014	0.210
22	0.160	0.270	0.653	0.757	2.00	1.16	1.64	0.860	0.653	0.035	0.023	0.210
23	0.160	0.270	0.653	0.757	1.80	1.00	1.48	0.860	0.653	0.035	0.023	0.210
24	0.160	0.390	0.653	0.757	1.80	1.16	1.48	0.860	0.653	0.023	0.023	0.210
25	0.160	0.653	0.653	0.757	2.00	1.16	1.32	0.860	0.550	0.023	0.023	0.210
26	0.160	0.860	0.653	0.757	2.20	1.00	1.16	1.00	0.550	0.023	0.023	0.160
27	0.160	1.48	0.757	0.757	2.20	1.00	1.16	0.860	0.550	0.023	0.023	0.129
28	0.160	1.32	1.16	0.757	2.00	0.860	1.16	0.860	0.550	0.023	0.023	0.129
29	0.160	1.16	1.00	0.653	-----	0.860	1.32	0.757	0.653	0.023	0.023	0.160
30	0.160	1.00	0.757	0.757	-----	0.860	1.32	0.653	0.653	0.023	0.014	0.160
31	0.210	-----	1.16	0.653	-----	0.860	-----	0.653	-----	0.023	0.014	-----
Maks.	0.390	2.00	1.64	3.40	6.20	4.00	2.00	2.00	1.00	0.653	0.052	0.210
Min.	0.035	0.160	0.470	0.653	0.550	0.757	0.757	0.653	0.550	0.014	0.003	0.014
Ortalama	0.243	0.392	0.719	0.794	1.53	1.52	1.28	1.03	0.715	0.258	0.019	0.086
LT/SN/Km2	4.10	6.61	12.1	13.4	25.8	25.6	21.5	17.3	12.0	4.35	0.312	1.44
AKIM mm.	11.0	17.1	32.4	35.8	62.4	68.7	55.9	46.3	31.2	11.6	0.836	3.74
MİL. M3	0.652	1.02	1.93	2.13	3.70	4.08	3.32	2.75	1.85	0.691	0.050	0.222

SU YILI (2006) YILLIK TOPLAM AKIM 22.40 MİLYON M3 377 MM. 12.0 LT/SN/Km2

12. Sakarya Havzasi

D12A176 Akgöl Çikisi K.Hasan Köp.

YERİ : **YUNAK ANKARA YOLUNUN 40.KM. K.HASAN KÖPRÜSÜNDEDİR**
41°49'54" Doğu - 38°57'32" Kuzey

YAĞIŞ ALANI : **1000,00 km2** **YAKLAŞIK KOT : 890 m**

GÖZLEM SÜRESİ : **01.10.1984 - 30.09.2006**

ORTALAMA AKIMLAR : **Gözlem süresinde 1.897 m3/sn. (14 Yıllık) 2006 Su yılında 1.193 m3/sn.**

ANLIK EN ÇOK VE EN AZ AKIMLAR:

2006 Su yılında anlık ençok akım	**:**	**4.06**	**m3/sn**	**13.02.2006**
2006 Su yılında anlık enaz akım	**:**	**0.248**	**m3/sn**	**16.08.2006**
Gözlem süresinde anlık ençok akım	**:**	**7.00**	**m3/sn**	**29.03.1999**
Gözlem süresinde anlık enaz akım	**:**	**0.000**	**m3/sn**	**01.10.1983**

İstasyon için kullanılmış anahtar bulunamadı.

Akımlar 01 Ekim 2005 'den 30 Eylül 2006' a kadar m3/sn olarak

Gün	Ekim	Kasım	Aralık	Ocak	Şubat	Mart	Nisan	Mayıs	Haziran	Temmuz	Ağustos	Eylül
01	1.05	0.880	1.10	1.23	1.52	2.25	1.59	0.648	1.40	0.626	0.396	0.433
02	1.16	0.880	1.10	1.23	1.52	2.40	1.59	0.760	1.40	0.626	0.396	0.590
03	1.26	1.03	1.10	1.23	1.52	2.40	1.59	0.968	1.40	0.540	0.396	0.590
04	1.26	1.34	1.10	1.31	1.64	2.40	1.59	1.18	1.40	0.540	0.396	0.590
05	1.37	1.46	0.980	1.40	1.76	2.25	1.49	1.80	1.31	0.540	0.359	0.530
06	1.47	1.46	0.980	1.40	2.00	2.25	1.38	1.80	1.31	0.540	0.359	0.530
07	1.37	1.46	0.980	1.52	2.00	2.25	1.38	1.80	1.23	0.499	0.322	0.470
08	1.26	1.46	0.980	1.52	2.24	2.10	1.28	1.70	1.23	0.457	0.322	0.470
09	1.05	1.34	0.980	1.64	2.48	2.10	1.07	1.49	1.23	0.416	0.322	0.590
10	1.05	1.34	1.10	1.64	2.48	2.10	1.07	1.49	1.23	0.416	0.285	0.590
11	1.05	1.34	1.22	1.64	2.60	1.95	1.18	1.49	1.23	0.416	0.322	0.620
12	1.26	1.22	1.22	1.76	3.30	1.95	1.18	1.49	1.23	0.416	0.322	0.620
13	1.26	1.22	1.22	1.76	3.87	1.80	1.18	1.49	1.23	0.374	0.322	0.707
14	1.26	1.22	1.22	1.76	3.68	1.70	1.18	1.28	1.23	0.333	0.285	0.707
15	1.26	1.10	1.22	1.64	3.68	1.70	1.38	1.28	1.14	0.333	0.285	0.707
16	1.37	1.10	1.34	1.64	3.30	1.59	1.38	1.28	1.06	0.333	0.248	0.707
17	0.880	0.980	1.46	1.64	3.00	1.80	1.38	1.18	1.06	0.333	0.248	0.707
18	0.880	0.980	1.46	1.88	3.00	1.95	1.28	1.18	1.06	0.291	0.248	0.620
19	0.793	1.10	1.46	1.88	2.70	2.10	1.07	1.18	1.06	0.291	0.322	0.590
20	0.793	1.22	1.46	2.00	2.70	2.10	0.968	1.07	1.06	0.291	0.359	0.590
21	0.793	1.22	1.58	2.00	2.70	2.40	0.968	0.968	0.970	0.291	0.359	0.620
22	0.793	1.22	1.70	2.12	2.40	2.40	0.968	0.864	0.884	0.590	0.359	0.620
23	0.793	1.22	1.70	2.36	2.40	2.40	0.864	0.864	0.884	0.590	0.396	0.707
24	0.793	1.22	1.70	2.36	2.40	2.25	0.864	0.864	0.884	0.470	0.396	0.499
25	0.880	1.22	1.06	2.24	2.40	2.10	0.864	0.704	0.712	0.470	0.433	0.626
26	0.880	1.10	1.06	2.00	2.40	1.80	0.704	0.704	0.626	0.433	0.396	0.626
27	0.880	1.10	1.06	2.00	2.10	1.70	0.592	0.704	0.626	0.433	0.396	0.540
28	0.880	1.10	1.06	1.76	2.10	1.70	0.536	0.648	0.626	0.396	0.396	0.712
29	0.880	1.10	1.06	1.64	-----	1.70	0.424	0.648	0.626	0.396	0.396	0.884
30	0.880	1.10	1.14	1.52	-----	1.59	0.424	0.648	0.626	0.396	0.396	0.970
31	0.880	-----	1.14	1.52	-----	1.59	-----	0.704	-----	0.396	0.396	-----
Maks.	1.47	1.46	1.70	2.36	4.06	2.40	1.59	1.80	1.64	0.626	0.433	1.06
Min.	0.793	0.880	0.980	1.23	1.52	1.59	0.424	0.648	0.626	0.291	0.248	0.396
Ortalama	1.05	1.19	1.22	1.72	2.50	2.02	1.11	1.13	1.07	0.435	0.349	0.625
LT/SN/Km2	1.05	1.19	1.22	1.72	2.50	2.02	1.11	1.13	1.07	0.435	0.349	0.625
AKIM mm.	2.80	3.09	3.28	4.60	6.04	5.42	2.89	3.01	2.76	1.16	0.936	1.62
MİL. M3	2.80	3.09	3.28	4.60	6.04	5.42	2.89	3.01	2.76	1.16	0.936	1.62

SU YILI (2006) YILLIK TOPLAM AKIM 37.61 MİLYON M3 38 MM. 1.2 LT/SN/Km2

12. Sakarya Havzasi

D12A177 HOCAKÖY DERE HOCAKÖY

YERİ : BURSA İLİ İNEGÖL İLÇESİ HOCAKÖY KÖYÜNÜN 500 M. MENBAINDADIR. (LİMNIGRAFLI .)
29°28'19" Doğu - 40°3'21" Kuzey

YAĞIŞ ALANI : 31,00 km2 **YAKLAŞIK KOT :** 363 m

GÖZLEM SÜRESİ : 23.10.1984 - 30.09.2006

ORTALAMA AKIMLAR : Gözlem süresinde 0.641 m3/sn. (20 Yıllık) 2006 Su yılında 0.849 m3/sn.

ANLIK EN ÇOK VE EN AZ AKIMLAR:

2006 Su yılında anlık ençok akım	:	13.7	m3/sn	03.03.2006
2006 Su yılında anlık enaz akım	:	0.007	m3/sn	07.09.2006
Gözlem süresinde anlık ençok akım	:	34.0	m3/sn	25.12.2001
Gözlem süresinde anlık enaz akım	:	0.000	m3/sn	31.10.1991

2. Anahtar Eğrisi (Seviyeler cm olarak)

Seviye	Akım	Seviye	Akım	Seviye	Akım	Seviye	Akım
13	0.001	48	4.8	83	19.6	118	38.2
20	0.072	55	7.1	90	23.1	126	42.5
27	0.481	62	9.9	97	26.9	133	46.5
34	1.4	69	12.9	105	30.8		
41	2.9	76	16.1	111	34.3		

Akımlar 01 Ekim 2005 'den 30 Eylül 2006' a kadar m3/sn olarak

Gün	Ekim	Kasım	Aralık	Ocak	Şubat	Mart	Nisan	Mayıs	Haziran	Temmuz	Ağustos	Eylül
01	0.058	0.120	0.476	1.40	0.860	3.15	1.76	1.94	0.476	0.120	0.035	0.035
02	0.080	0.120	0.476	1.22	0.860	3.00	1.76	1.76	0.476	0.120	0.035	0.080
03	0.120	0.120	0.476	1.04	0.860	6.87	1.58	1.76	0.380	0.120	0.035	0.058
04	0.120	0.120	0.476	0.860	0.860	4.84	1.58	1.04	0.300	0.160	0.035	0.058
05	0.080	0.230	0.380	0.860	0.668	3.60	1.76	0.860	0.230	0.160	0.035	0.058
06	0.080	0.300	0.380	0.860	0.380	2.80	1.58	0.860	0.230	0.120	0.035	0.058
07	0.080	0.380	0.380	0.764	0.668	2.30	2.45	0.764	0.230	0.120	0.035	0.035
08	0.080	0.230	0.380	0.860	0.764	2.45	4.00	0.860	0.230	0.120	0.035	0.035
09	0.080	0.230	0.380	0.764	0.764	2.12	4.20	0.860	0.380	0.080	0.035	0.035
10	0.080	0.160	0.380	0.764	1.94	2.12	4.00	0.860	0.300	0.080	0.035	0.035
11	0.080	0.160	0.380	0.764	3.80	2.12	4.00	0.860	0.300	0.120	0.035	0.035
12	0.080	0.160	0.380	0.764	2.12	3.45	4.00	0.860	0.230	0.080	0.035	0.035
13	0.080	0.160	0.380	0.764	1.58	3.00	4.00	0.860	0.300	0.080	0.035	0.035
14	0.080	0.160	0.380	0.764	1.40	2.60	3.80	0.860	0.380	0.080	0.035	0.035
15	0.080	0.300	0.380	0.764	1.22	2.30	3.45	0.860	0.476	0.080	0.035	0.035
16	0.080	0.230	0.380	0.764	1.04	2.12	3.15	0.860	0.380	0.120	0.035	0.035
17	0.120	0.160	0.380	0.764	1.04	1.94	3.00	0.860	0.300	0.080	0.035	0.035
18	0.120	0.668	0.668	0.764	1.76	1.76	3.00	0.860	0.300	0.080	0.035	0.035
19	0.120	0.380	1.04	1.04	2.30	1.58	3.00	0.764	0.300	0.080	0.035	0.058
20	0.120	0.860	0.764	1.04	2.60	1.58	3.15	0.764	0.230	0.080	0.035	0.080
21	0.120	0.476	0.764	0.860	2.45	1.40	3.30	0.764	0.230	0.058	0.035	0.230
22	0.120	0.380	0.764	0.860	2.30	1.22	3.15	0.764	0.230	0.058	0.035	0.160
23	0.120	0.380	0.668	0.860	2.30	1.58	2.80	0.668	0.230	0.058	0.035	0.160
24	0.120	0.572	0.572	0.860	2.30	2.12	2.80	0.572	0.230	0.058	0.035	0.160
25	0.120	0.860	0.572	0.860	3.15	2.12	2.45	0.572	0.160	0.058	0.035	0.160
26	0.120	1.04	0.572	0.860	3.60	1.94	2.12	0.572	0.160	0.058	0.035	0.120
27	0.120	1.04	0.572	0.860	3.45	1.76	1.94	0.476	0.160	0.058	0.035	0.120
28	0.120	0.764	0.668	0.860	3.15	1.58	1.94	0.476	0.160	0.058	0.024	0.120
29	0.120	0.764	1.04	0.860	-----	1.58	1.94	0.476	0.160	0.035	0.024	0.380
30	0.120	0.572	0.860	0.860	-----	1.94	1.94	0.476	0.160	0.035	0.024	0.230
31	0.160	-----	1.58	0.860	-----	1.94	-----	0.476	-----	0.035	0.024	-----
Maks.	0.160	1.94	2.30	1.76	7.67	13.7	4.84	1.94	0.476	0.230	0.058	1.04
Min.	0.058	0.120	0.380	0.764	0.160	1.22	1.22	0.300	0.120	0.035	0.024	0.007
Ortalama	0.103	0.403	0.579	0.872	1.79	2.42	2.79	0.847	0.277	0.085	0.034	0.092
LT/SN/Km2	3.31	13.0	18.7	28.1	57.8	77.9	89.9	27.3	8.93	2.76	1.08	2.95
AKIM mm.	8.86	33.7	50.0	75.4	140.	209.	233.	73.2	23.2	7.38	2.90	7.65
MİL. M3	0.275	1.05	1.55	2.34	4.34	6.47	7.22	2.27	0.718	0.229	0.090	0.237

SU YILI (2006) YILLIK TOPLAM AKIM 26.79 MİLYON M3 864 MM. 27.4 LT/SN/Km2

12. Sakarya Havzasi

D12A181 PORSUK Ç. ÇALÇA (Y.BOSNA)

YERİ : **KÜTAHYA ESKİŞEHİR KARAYOLUNUN 10 KM SİNDEKİ AZOT FABRİKASINDAN SAĞA DÖNÜLEN YOLUN 1KM MESAFEDEKİ YENİBOSNA KÖYÜ KÖPRÜ-**
30°8'0" Doğu - 39°28'0" Kuzey

YAĞIŞ ALANI : **3810.50 km2** **YAKLAŞIK KOT : 912 m**

GÖZLEM SÜRESİ : **01.10.1985 - 30.09.2006**

ORTALAMA AKIMLAR : **Gözlem süresinde 5.243 m3/sn. (19 Yıllık) 2006 Su yılında 8.085 m3/sn.**

ANLIK EN ÇOK VE EN AZ AKIMLAR:

2006 Su yılında anlık ençok akım	**:**	**49.0**	**m3/sn**	**28.02.2006**
2006 Su yılında anlık enaz akım	**:**	**1.55**	**m3/sn**	**03.08.2006**
Gözlem süresinde anlık ençok akım	**:**	**55.9**	**m3/sn**	**27.02.1999**
Gözlem süresinde anlık enaz akım	**:**	**0.000**	**m3/sn**	**06.07.1990**

Akımlar 01 Ekim 2005 'den 30 Eylül 2006' a kadar m3/sn olarak

Gün	Ekim	Kasım	Aralık	Ocak	Şubat	Mart	Nisan	Mayıs	Haziran	Temmuz	Ağustos	Eylül
01	2.51	3.07	3.59	4.33	5.05	43.1	20.0	11.5	4.04	2.34	1.62	2.86
02	2.86	3.07	3.59	4.33	4.62	36.7	19.3	11.1	4.04	2.25	1.62	3.28
03	2.86	3.38	3.59	4.62	3.69	40.3	19.3	10.8	4.04	1.99	1.55	3.28
04	2.86	3.38	3.48	4.62	3.90	40.3	18.4	10.2	3.90	2.16	1.55	3.07
05	2.86	3.17	3.59	5.83	3.90	43.1	18.4	10.2	4.19	2.16	1.55	2.96
06	2.86	3.17	3.59	4.76	4.62	42.2	18.0	10.9	4.19	2.16	1.55	2.96
07	2.86	3.28	3.48	4.91	4.91	34.6	17.5	12.1	3.07	2.08	1.55	2.96
08	2.77	3.17	3.38	5.05	4.76	28.8	17.1	12.1	3.17	1.99	1.55	2.96
09	2.86	3.28	3.48	5.20	4.91	27.3	16.6	12.4	3.17	1.99	1.62	2.96
10	2.96	3.07	3.48	5.05	6.47	28.2	16.6	12.6	3.80	1.92	2.96	2.96
11	2.96	3.07	3.38	4.48	12.6	26.0	16.6	11.7	3.90	1.92	2.96	3.07
12	2.86	3.07	3.48	4.33	13.6	25.8	16.0	10.9	3.90	1.92	2.96	3.17
13	2.96	3.07	3.48	4.04	22.4	24.9	15.1	10.4	3.38	1.99	2.96	2.96
14	2.69	2.96	3.38	4.04	25.3	25.3	13.8	10.0	3.38	1.99	2.96	2.96
15	2.69	3.07	3.48	4.04	20.7	27.3	13.6	10.0	3.59	1.84	2.86	3.07
16	2.69	3.17	3.69	3.90	17.8	31.4	13.9	10.0	3.69	1.92	2.86	3.17
17	2.69	3.07	3.90	3.80	16.2	29.4	14.1	9.88	3.69	1.92	2.86	3.28
18	2.69	3.28	3.59	4.04	16.4	27.3	13.6	9.71	4.76	1.92	2.96	3.28
19	2.96	3.17	4.76	5.05	19.1	26.2	12.8	9.07	3.69	2.16	2.69	4.04
20	3.07	3.69	4.33	6.31	25.8	24.4	11.3	9.23	2.96	1.99	2.69	4.04
21	2.96	3.80	4.04	6.80	33.8	23.6	11.3	9.07	2.69	1.77	2.69	4.91
22	2.96	3.80	4.33	8.90	38.3	22.2	11.5	8.74	2.77	1.84	2.77	5.66
23	3.07	3.80	4.48	6.80	36.7	21.6	11.9	7.93	2.51	1.84	2.77	4.62
24	2.96	3.80	4.33	5.34	34.6	21.6	12.3	7.45	2.51	1.84	2.77	3.59
25	2.86	3.80	4.19	4.19	33.4	22.4	12.6	6.47	2.08	1.92	2.77	3.90
26	2.86	5.83	4.19	4.76	37.5	23.8	12.1	5.99	1.99	1.69	2.86	3.69
27	2.86	4.48	4.62	4.76	43.1	23.8	10.9	6.47	2.08	1.69	2.77	3.59
28	2.96	4.19	4.62	5.50	45.3	22.4	10.6	6.15	2.86	1.69	2.77	3.80
29	2.86	3.80	4.48	5.99	-----	21.3	10.8	4.62	2.43	1.62	2.77	5.05
30	2.96	3.59	4.33	5.34	-----	20.7	10.9	4.33	2.25	1.62	2.77	4.48
31	2.96	-----	4.76	5.20	-----	20.4	-----	4.19	-----	1.62	2.77	-----
Maks.	3.28	6.80	5.99	10.2	49.0	49.0	20.7	13.6	5.66	2.60	3.69	6.64
Min.	2.51	2.86	3.07	3.80	3.69	20.4	10.2	3.80	1.84	1.62	1.55	2.77
Ortalama	2.86	3.49	3.91	5.04	19.3	28.3	14.6	9.23	3.29	1.93	2.46	3.55
LT/SN/Km2	0.752	0.915	1.03	1.32	5.06	7.42	3.82	2.42	0.864	0.506	0.646	0.932
AKIM mm.	2.01	2.37	2.75	3.54	12.2	19.9	9.91	6.49	2.24	1.35	1.73	2.42
MİL. M3	7.67	9.03	10.5	13.5	46.6	75.7	37.7	24.7	8.53	5.16	6.60	9.21

SU YILI (2006) YILLIK TOPLAM AKIM 254.90 MİLYON M3 67 MM. 2.1 LT/SN/Km2

12. Sakarya Havzasi

D12A182 PÜRTEK D. MEMİK

YERİ : **ESKİŞEHİR-SİVRİHİSAR İLÇESİNE BAĞLI MEMİK KÖYÜNE VARILIRMEMİK ZEYKÖY ARASI 14.KM DEDİR.**
33°30'0" Doğu - 33°33'0" Kuzey

YAĞIŞ ALANI : **177.10 km2** **YAKLAŞIK KOT : 960 m**

GÖZLEM SÜRESİ : **01.10.1985 - 30.09.2006**

ORTALAMA AKIMLAR : **Gözlem süresinde 0.093 m3/sn. (16 Yıllık) 2006 Su yılında 0.043 m3/sn.**

ANLIK EN ÇOK VE EN AZ AKIMLAR:

2006 Su yılında anlık ençok akım	**:**	**0.160 m3/sn**	**21.02.2006**
2006 Su yılında anlık enaz akım	**:**	**0.003 m3/sn**	**31.08.2006**
Gözlem süresinde anlık ençok akım	**:**	**4.70 m3/sn**	**05.10.1991**
Gözlem süresinde anlık enaz akım	**:**	**0.000 m3/sn**	**02.08.1989**

Akımlar 01 Ekim 2005 'den 30 Eylül 2006' a kadar m3/sn olarak

Gün	Ekim	Kasım	Aralık	Ocak	Şubat	Mart	Nisan	Mayıs	Haziran	Temmuz	Ağustos	Eylül
01	0.017	0.027	0.040	0.056	0.040	0.094	0.040	0.040	0.017	0.074	0.008	0.008
02	0.017	0.027	0.040	0.056	0.056	0.094	0.056	0.056	0.017	0.074	0.008	0.008
03	0.017	0.027	0.040	0.056	0.040	0.094	0.056	0.040	0.017	0.074	0.008	0.003
04	0.017	0.027	0.040	0.056	0.056	0.094	0.056	0.040	0.027	0.056	0.008	0.003
05	0.017	0.040	0.040	0.056	0.056	0.094	0.056	0.056	0.027	0.056	0.008	0.008
06	0.017	0.040	0.040	0.056	0.056	0.094	0.056	0.074	0.027	0.056	0.008	0.008
07	0.017	0.040	0.040	0.056	0.056	0.094	0.056	0.074	0.017	0.056	0.008	0.008
08	0.017	0.040	0.040	0.056	0.056	0.094	0.056	0.074	0.017	0.056	0.003	0.008
09	0.017	0.040	0.040	0.056	0.056	0.094	0.056	0.074	0.017	0.056	0.003	0.008
10	0.017	0.040	0.040	0.056	0.056	0.094	0.056	0.056	0.027	0.056	0.003	0.008
11	0.017	0.040	0.040	0.056	0.115	0.094	0.056	0.056	0.027	0.040	0.008	0.008
12	0.017	0.040	0.040	0.056	0.140	0.094	0.040	0.056	0.017	0.056	0.008	0.008
13	0.017	0.040	0.040	0.056	0.115	0.094	0.040	0.056	0.027	0.056	0.008	0.008
14	0.017	0.040	0.040	0.056	0.094	0.094	0.040	0.056	0.027	0.056	0.008	0.017
15	0.027	0.040	0.040	0.056	0.094	0.094	0.040	0.056	0.040	0.056	0.008	0.017
16	0.027	0.040	0.040	0.056	0.074	0.094	0.056	0.056	0.027	0.056	0.008	0.008
17	0.027	0.040	0.056	0.056	0.074	0.094	0.056	0.056	0.027	0.056	0.008	0.008
18	0.027	0.040	0.040	0.056	0.074	0.094	0.040	0.056	0.027	0.056	0.008	0.008
19	0.040	0.027	0.040	0.056	0.115	0.094	0.056	0.040	0.040	0.040	0.008	0.008
20	0.056	0.027	0.040	0.056	0.140	0.094	0.040	0.040	0.040	0.040	0.008	0.008
21	0.040	0.040	0.040	0.056	0.160	0.094	0.040	0.027	0.027	0.027	0.008	0.017
22	0.027	0.040	0.040	0.040	0.140	0.094	0.040	0.040	0.040	0.027	0.003	0.017
23	0.027	0.040	0.040	0.040	0.140	0.094	0.040	0.027	0.017	0.027	0.008	0.017
24	0.027	0.040	0.040	0.056	0.115	0.094	0.040	0.040	0.017	0.027	0.008	0.017
25	0.017	0.040	0.040	0.056	0.115	0.074	0.040	0.027	0.040	0.027	0.008	0.074
26	0.027	0.040	0.040	0.040	0.115	0.056	0.040	0.040	0.008	0.027	0.017	0.040
27	0.027	0.040	0.040	0.040	0.115	0.056	0.040	0.040	0.008	0.027	0.008	0.027
28	0.027	0.040	0.040	0.040	0.094	0.056	0.040	0.040	0.017	0.027	0.003	0.027
29	0.027	0.040	0.040	0.040	-----	0.056	0.027	0.027	0.027	0.027	0.003	0.094
30	0.027	0.040	0.056	0.040	-----	0.056	0.027	0.027	0.074	0.017	0.008	0.040
31	0.027	-----	0.056	0.040	-----	0.056	-----	0.017	-----	0.017	0.003	-----
Maks.	0.056	0.040	0.056	0.056	0.160	0.094	0.056	0.074	0.074	0.074	0.017	0.094
Min.	0.017	0.027	0.040	0.040	0.040	0.056	0.027	0.017	0.008	0.017	0.003	0.003
Ortalama	0.024	0.037	0.042	0.052	0.091	0.086	0.046	0.047	0.026	0.045	0.007	0.018
LT/SN/Km2	0.135	0.211	0.235	0.293	0.516	0.486	0.260	0.267	0.148	0.256	0.040	0.101
AKIM mm.	0.362	0.547	0.628	0.784	1.25	1.30	0.674	0.714	0.382	0.684	0.108	0.262
MİL. M3	0.064	0.097	0.111	0.139	0.221	0.230	0.119	0.126	0.068	0.121	0.019	0.046

SU YILI (2006) YILLIK TOPLAM AKIM 1.36 MİLYON M3 8 MM. 0.2 LT/SN/Km2

12. Sakarya Havzasi

D12A184 KUNDUZLAR BRJ. BARAJ ÇIKIŞ

YERİ : **ESKİŞEHİR-SEYİTGAZİDEN KIRKAYA 64 KMSİNDEN YOL İKİYE AYRILIRYOL KAVŞAĞINDAN SONRAKİ BARAJIN 200 MT ALTINDADIR.**
30°35'0" Doğu - 39°21'0" Kuzey

YAĞIŞ ALANI : **406.00 km2** **YAKLAŞIK KOT : 5857 m**

GÖZLEM SÜRESİ : **01.12.1985 - 30.09.2006**

ORTALAMA AKIMLAR : **Gözlem süresinde 0.849 m3/sn. (17 Yıllık) 2006 Su yılında 0.771 m3/sn.**

ANLIK EN ÇOK VE EN AZ AKIMLAR:

2006 Su yılında anlık ençok akım	:	**5.00**	**m3/sn**	**19.04.2006**
2006 Su yılında anlık enaz akım	:	**0.000**	**m3/sn**	**01.10.2005**
Gözlem süresinde anlık ençok akım	:	**12.5**	**m3/sn**	**26.03.1987**
Gözlem süresinde anlık enaz akım	:	**0.000**	**m3/sn**	**22.10.1986**

Akımlar 01 Ekim 2005 'den 30 Eylül 2006' a kadar m3/sn olarak

Gün	Ekim	Kasım	Aralık	Ocak	Şubat	Mart	Nisan	Mayıs	Haziran	Temmuz	Ağustos	Eylül
01	KURU	KURU	0.019	0.066	0.066	0.135	0.135	4.00	2.60	2.90	0.220	0.066
02	KURU	KURU	0.019	0.066	0.066	0.135	0.135	4.00	2.60	2.90	0.220	0.066
03	KURU	KURU	0.019	0.066	0.066	0.135	0.135	4.00	2.60	2.90	0.220	0.066
04	KURU	KURU	0.019	0.066	0.066	0.135	0.135	4.00	2.60	2.90	0.220	0.066
05	KURU	KURU	0.019	0.066	0.066	0.135	0.066	4.00	2.60	2.90	0.220	0.066
06	KURU	KURU	0.019	0.066	0.066	0.135	0.066	3.70	0.560	2.90	0.220	0.066
07	KURU	KURU	0.019	0.066	0.066	0.135	0.066	3.40	0.019	2.90	0.220	0.066
08	KURU	KURU	0.019	0.066	0.066	0.135	0.066	3.40	0.019	2.90	0.220	0.066
09	KURU	KURU	0.019	0.066	0.066	0.135	0.066	3.40	0.019	2.90	0.220	0.066
10	KURU	KURU	0.019	0.066	0.066	0.135	0.066	3.40	0.019	2.90	0.220	0.066
11	KURU	KURU	0.019	0.066	0.066	0.135	0.066	2.90	0.560	2.90	0.220	0.066
12	KURU	KURU	0.019	0.066	0.066	0.135	0.019	2.90	2.20	2.90	0.220	0.066
13	KURU	KURU	0.019	0.066	0.066	0.135	0.019	2.90	2.20	2.90	0.220	0.066
14	KURU	0.019	0.019	0.066	0.066	0.135	0.019	2.90	1.95	2.90	0.220	0.066
15	KURU	0.019	0.019	0.066	0.066	0.135	0.019	2.60	1.15	2.90	0.220	0.066
16	KURU	0.019	0.019	0.066	0.066	0.135	0.019	1.50	0.066	2.90	0.560	0.066
17	KURU	0.019	0.019	0.066	0.066	0.135	0.019	1.15	1.70	2.90	0.320	0.066
18	KURU	0.019	0.019	0.066	0.066	0.135	2.60	1.15	2.60	2.90	0.135	0.066
19	KURU	0.019	0.019	0.066	0.066	0.135	4.00	1.15	2.60	2.90	0.135	0.066
20	KURU	0.019	0.019	0.066	0.135	0.135	5.00	1.15	2.60	2.90	0.135	0.066
21	KURU	0.019	0.019	0.066	0.135	0.135	5.00	1.15	2.60	2.90	0.066	0.066
22	KURU	0.019	0.019	0.066	0.135	0.135	5.00	0.560	2.60	2.90	0.066	0.066
23	KURU	0.019	0.019	0.066	0.135	0.135	5.00	0.066	2.60	3.20	0.066	0.066
24	KURU	0.019	0.019	0.066	0.135	0.135	5.00	0.066	2.60	3.20	0.066	0.066
25	KURU	0.019	0.019	0.066	0.135	0.135	5.00	0.066	2.60	1.95	0.066	0.066
26	KURU	0.019	0.019	0.066	0.135	0.135	5.00	0.066	2.60	1.15	0.066	0.066
27	KURU	0.019	0.019	0.066	0.135	0.135	5.00	0.066	2.90	1.15	0.066	0.066
28	KURU	0.019	0.019	0.066	0.135	0.135	5.00	0.560	2.90	1.35	0.066	0.066
29	KURU	0.019	0.066	0.066	-----	0.135	4.70	2.20	2.90	0.560	0.066	0.066
30	KURU	0.019	0.066	0.066	-----	0.135	4.00	2.60	2.90	0.220	0.066	0.066
31	KURU	-----	0.066	0.066	-----	0.135	-----	2.60	-----	0.220	0.066	-----
Maks.	KURU	0.019	0.066	0.066	0.135	0.135	5.00	4.00	2.90	3.20	0.560	0.066
Min.	KURU	KURU	0.019	0.066	0.066	0.135	KURU	0.066	0.019	0.220	0.066	0.066
Ortalama	KURU	0.011	0.024	0.066	0.088	0.135	2.05	2.18	1.95	2.48	0.171	0.066
LT/SN/Km2	0.000	0.027	0.058	0.163	0.217	0.333	5.04	5.37	4.80	6.10	0.422	0.163
AKIM mm.	0.000	0.069	0.155	0.435	0.525	0.891	13.1	14.4	12.4	16.3	1.13	0.421
MİL. M3	0.000	0.028	0.063	0.177	0.213	0.362	5.31	5.84	5.05	6.64	0.459	0.171

SU YILI (2006) YILLIK TOPLAM AKIM 24.31 MİLYON M3 60 MM. 1.9 LT/SN/Km2

12. Sakarya Havzasi

D12A185 AKİN DERESI GEMİŞ

YERİ : **ESKİŞEHİR-KIRKAYA 3.KM KALA SAĞA DÖNER 4 KM DEN SONRA AKİNKÖYÜNDEN GEÇEREK 3 KM SONRA GEMİŞ KÖYÜNÜN ÇIKIŞINDAN SOLA**
30°30'0" Doğu - 39°20'0" Kuzey

YAĞIŞ ALANI : **218.23 km2** **YAKLAŞIK KOT : 1742 m**

GÖZLEM SÜRESİ : **15.12.1985 - 30.09.2006**

ORTALAMA AKIMLAR : **Gözlem süresinde 0.508 m3/sn. (19 Yıllık) 2006 Su yılında 0.426 m3/sn.**

ANLIK EN ÇOK VE EN AZ AKIMLAR:

2006 Su yılında anlık ençok akım	:	**8.80**	**m3/sn**	**03.03.2006**
2006 Su yılında anlık enaz akım	:	**0.019**	**m3/sn**	**21.07.2006**
Gözlem süresinde anlık ençok akım	:	**88.0**	**m3/sn**	**08.04.1992**
Gözlem süresinde anlık enaz akım	:	**0.000**	**m3/sn**	**01.10.1985**

Akımlar 01 Ekim 2005 'den 30 Eylül 2006' a kadar m3/sn olarak

Gün	Ekim	Kasım	Aralık	Ocak	Şubat	Mart	Nisan	Mayıs	Haziran	Temmuz	Ağustos	Eylül
01	0.050	0.134	0.086	0.050	0.316	2.60	1.20	0.552	0.483	0.050	0.019	0.050
02	0.050	0.134	0.086	0.050	0.316	2.76	0.992	0.552	0.483	0.483	0.019	0.050
03	0.050	0.134	0.086	0.050	0.316	8.80	0.992	0.552	0.483	0.245	0.019	0.050
04	0.050	0.186	0.086	0.050	0.316	3.40	0.992	0.552	0.483	0.186	0.019	0.050
05	0.050	0.186	0.086	0.050	0.316	2.38	0.992	0.552	0.483	0.186	0.019	0.019
06	0.050	0.186	0.086	0.134	0.316	2.27	0.992	0.552	0.483	0.186	0.019	0.019
07	0.050	0.186	0.086	0.245	0.316	2.16	0.904	0.552	0.186	0.186	0.019	0.050
08	0.050	0.186	0.086	0.245	0.316	2.49	0.816	0.552	0.086	0.398	0.019	0.050
09	0.050	0.186	0.086	0.245	0.316	1.94	0.816	0.483	0.086	1.30	0.019	0.050
10	0.050	0.186	0.086	0.245	0.245	1.72	0.816	0.483	0.086	1.30	0.019	0.050
11	0.050	0.186	0.086	0.245	0.245	1.61	0.728	0.483	0.086	1.20	0.019	0.050
12	0.050	0.186	0.086	0.245	0.186	1.61	0.728	0.483	0.086	1.20	0.050	0.050
13	0.050	0.186	0.086	0.245	0.186	1.83	0.728	0.483	0.086	1.20	0.050	0.050
14	0.050	0.134	0.086	0.245	0.186	1.94	0.728	0.483	0.086	1.20	0.019	0.050
15	0.086	0.134	0.086	0.245	0.186	1.72	0.728	0.483	0.086	1.09	0.019	0.050
16	0.086	0.134	0.086	0.245	0.186	1.50	0.728	0.483	0.086	1.09	0.050	0.050
17	0.086	0.134	0.086	0.245	0.186	1.30	0.728	0.483	0.086	1.09	0.019	0.050
18	0.086	0.134	0.086	0.245	0.134	1.30	0.640	0.483	0.086	1.09	0.050	0.050
19	0.086	0.134	0.086	0.186	0.134	1.30	0.640	0.483	0.086	0.992	0.050	0.050
20	0.134	0.134	0.086	0.186	0.186	0.992	0.640	0.483	0.086	0.050	0.019	0.086
21	0.134	0.134	0.086	0.245	0.552	0.904	0.640	0.483	0.086	0.019	0.019	0.134
22	0.134	0.134	0.134	0.245	0.904	1.09	0.640	0.483	0.086	0.050	0.019	0.134
23	0.134	0.086	0.086	0.245	1.09	1.61	0.640	0.483	0.086	0.050	0.019	0.134
24	0.134	0.086	0.134	0.245	1.20	2.27	0.640	0.483	0.086	0.050	0.019	0.134
25	0.134	0.086	0.086	0.245	2.05	2.05	0.552	0.483	0.086	0.050	0.019	0.134
26	0.134	0.086	0.134	0.245	2.27	1.72	0.552	0.483	0.086	0.050	0.019	0.134
27	0.134	0.086	0.086	0.245	2.05	1.50	0.552	0.483	0.086	0.050	0.019	0.134
28	0.134	0.086	0.086	0.245	1.20	1.40	0.552	0.483	0.086	0.050	0.019	0.134
29	0.134	0.086	0.050	0.245	-----	1.30	0.552	0.483	0.050	0.050	0.019	0.134
30	0.134	0.086	0.050	0.245	-----	1.20	0.552	0.483	0.050	0.019	0.019	0.134
31	0.134	-----	0.050	0.316	-----	1.30	-----	0.483	-----	0.050	0.019	-----
Maks.	0.134	0.186	0.134	0.316	2.27	8.80	1.20	0.552	0.483	1.30	0.050	0.134
Min.	0.050	0.086	0.050	0.050	0.134	0.904	0.552	0.483	0.050	0.019	0.019	0.019
Ortalama	0.088	0.139	0.087	0.208	0.579	2.00	0.747	0.501	0.166	0.491	0.024	0.077
LT/SN/Km2	0.405	0.635	0.399	0.955	2.65	9.16	3.42	2.29	0.762	2.25	0.110	0.353
AKIM mm.	1.08	1.65	1.07	2.56	6.42	24.5	8.87	6.15	1.98	6.02	0.295	0.916
MİL. M3	0.237	0.359	0.233	0.558	1.40	5.35	1.94	1.34	0.431	1.31	0.064	0.200

SU YILI (2006) YILLIK TOPLAM AKIM 13.42 MİLYON M3 62 MM. 2.0 LT/SN/Km2

12. Sakarya Havzasi

D12A186 ÇARK S. REG ÇİKIS

YERİ : ADAPAZARI ÇARKSUYU REG SAPAĞINA 11.KM MESAFEDEDİR.
30°12'0" Doğu - 40°43'0" Kuzey

YAĞIŞ ALANI : 252.00 km2 **YAKLAŞIK KOT :** 132 m

GÖZLEM SÜRESİ : 01.10.1985 - 30.09.2006

ORTALAMA AKIMLAR : Gözlem süresinde 4.006 m3/sn. (13 Yıllık) 2006 Su yılında 3.806 m3/sn.

ANLIK EN ÇOK VE EN AZ AKIMLAR:

2006 Su yılında anlık ençok akım	:	13.5	m3/sn	28.03.2006
2006 Su yılında anlık enaz akım	:	0.012	m3/sn	01.10.2005
Gözlem süresinde anlık ençok akım	:	16.8	m3/sn	10.03.2005
Gözlem süresinde anlık enaz akım	:	0.004	m3/sn	17.09.2005

5. Anahtar Eğrisi (Seviyeler cm olarak)

Seviye	Akım	Seviye	Akım	Seviye	Akım	Seviye	Akım
60	0.003	100	0.169	155	2.2	262	19.9
66	0.007	109	0.304	173	3.8	280	24.3
70	0.012	119	0.524	193	6.2	306	30.0
80	0.034	130	0.886	220	11.3		
90	0.074	142	1.4	250	17.6		

Akımlar 01 Ekim 2005 'den 30 Eylül 2006' a kadar m3/sn olarak

Gün	Ekim	Kasım	Aralık	Ocak	Şubat	Mart	Nisan	Mayıs	Haziran	Temmuz	Ağustos	Eylül
01	0.012	0.054	3.96	5.80	9.29	11.3	13.3	1.61	0.111	0.129	0.079	0.051
02	0.016	0.050	3.96	5.80	9.29	11.4	13.3	0.739	0.096	0.120	0.079	0.045
03	0.016	0.050	3.96	5.67	9.11	11.6	13.3	0.713	0.102	0.111	0.074	0.045
04	0.016	0.050	3.96	5.67	8.93	11.8	13.3	0.713	0.102	0.102	0.074	0.045
05	0.023	0.050	3.96	5.67	8.93	12.0	13.1	0.939	0.102	0.102	0.068	0.045
06	0.023	0.054	3.96	5.67	8.93	12.0	13.1	1.34	0.102	0.091	0.096	0.051
07	0.023	0.054	3.96	5.67	8.93	12.0	13.1	1.34	0.102	0.079	0.068	0.079
08	0.023	0.062	3.96	5.67	9.47	12.1	13.1	1.34	0.102	0.079	0.062	0.062
09	0.025	0.062	3.96	5.67	9.64	12.6	13.1	1.34	0.102	0.079	0.056	0.045
10	0.027	0.054	3.96	5.67	9.64	12.7	12.9	1.34	0.102	0.079	0.056	0.045
11	0.030	0.050	3.96	5.67	9.82	12.7	12.9	1.34	0.102	0.079	0.056	0.051
12	0.034	0.046	4.21	5.67	10.0	12.7	12.7	1.34	0.111	0.079	0.056	0.051
13	0.042	0.046	4.21	5.67	10.1	12.7	12.7	1.34	0.120	0.079	0.085	0.056
14	0.046	0.141	4.21	5.67	10.1	12.9	12.7	1.34	0.120	0.079	0.074	0.062
15	0.050	1.38	4.21	5.67	10.1	13.3	12.7	0.477	0.111	0.079	0.051	0.062
16	0.050	1.55	4.21	5.67	10.1	13.3	12.6	0.173	0.102	0.079	0.045	0.062
17	0.058	1.50	4.21	5.67	10.1	13.3	10.4	0.182	0.096	0.079	0.045	0.062
18	0.066	1.50	4.09	5.67	10.6	13.3	8.58	0.182	0.096	0.074	0.045	0.062
19	0.070	1.50	4.33	5.67	10.6	13.3	8.22	0.182	0.096	0.074	0.045	0.062
20	0.103	1.50	4.57	5.80	10.6	13.3	8.22	0.182	0.096	0.074	0.045	0.062
21	0.070	1.55	4.45	5.92	10.7	13.3	8.22	0.173	0.102	0.074	0.045	0.062
22	0.050	1.61	4.33	5.92	10.7	13.3	8.22	0.173	0.102	0.074	0.045	0.062
23	0.046	1.61	4.33	7.14	10.9	13.3	8.22	0.155	0.096	0.074	0.045	0.062
24	0.042	2.65	4.33	8.76	10.9	13.3	6.32	0.155	0.091	0.079	0.045	0.062
25	0.042	3.96	4.33	8.93	10.9	13.3	4.94	0.147	0.091	0.079	0.045	0.096
26	0.042	3.96	4.33	9.29	11.0	13.3	4.70	0.138	0.091	0.079	0.045	0.129
27	0.042	3.96	5.06	9.29	11.3	13.3	4.45	0.138	0.091	0.079	0.045	0.129
28	0.042	3.96	5.80	9.29	11.3	13.3	3.64	0.138	0.091	0.079	0.045	0.129
29	0.046	3.96	5.80	9.29	-----	13.5	2.32	0.129	0.129	0.079	0.051	0.129
30	0.050	3.96	5.80	9.29	-----	13.3	2.24	0.129	0.129	0.079	0.051	0.129
31	0.054	-----	5.80	9.29	-----	13.3	-----	0.120	-----	0.079	0.051	-----
Maks.	0.122	3.96	5.92	9.29	11.4	13.5	13.3	2.24	0.155	0.129	0.129	0.129
Min.	0.012	0.046	3.31	5.67	8.93	11.3	2.24	0.111	0.079	0.074	0.042	0.045
Ortalama	0.041	1.36	4.39	6.65	10.1	12.8	9.89	0.637	0.103	0.084	0.057	0.070
LT/SN/Km2	0.164	5.41	17.4	26.4	40.0	50.8	39.2	2.53	0.408	0.333	0.227	0.277
AKIM mm.	0.439	14.0	46.7	70.7	96.7	136.	102.	6.77	1.06	0.891	0.608	0.718
MİL. M3	0.111	3.54	11.8	17.8	24.4	34.3	25.6	1.71	0.267	0.225	0.153	0.181

SU YILI (2006) YILLIK TOPLAM AKIM 120.09 MİLYON M3 477 MM. 15.1 LT/SN/Km2

12. Sakarya Havzasi

D12A188 NAL DERESİ YAKAPINAR

YERİ : **NALLIHAN-GÖYNÜK YOLUNUN 6.KM SİNDE NALTUR BENZİN İSTASYONUNUN ARKASINDA NAL DERESİ ÜZERİNDEDİR.**
31°20'32" Doğu - 40°14'23" Kuzey

YAĞIŞ ALANI : **618.00 km2** **YAKLAŞIK KOT : 662 m**

GÖZLEM SÜRESİ : **24.11.1987 - 30.09.2006**

ORTALAMA AKIMLAR : **Gözlem süresinde 1.489 m3/sn. (19 Yıllık) 2006 Su yılında 1.337 m3/sn.**

ANLIK EN ÇOK VE EN AZ AKIMLAR:

2006 Su yılında anlık ençok akım	:	**9.92**	**m3/sn**	**27.03.2006**
2006 Su yılında anlık enaz akım	:	**0.150**	**m3/sn**	**30.07.2006**
Gözlem süresinde anlık ençok akım	:	**58.0**	**m3/sn**	**16.08.1991**
Gözlem süresinde anlık enaz akım	:	**0.000**	**m3/sn**	**01.11.1987**

İstasyon için kullanılmış anahtar bulunamadı.

Akımlar 01 Ekim 2005 'den 30 Eylül 2006' a kadar m3/sn olarak

Gün	Ekim	Kasım	Aralık	Ocak	Şubat	Mart	Nisan	Mayıs	Haziran	Temmuz	Ağustos	Eylül
01	0.440	0.535	0.640	0.880	0.535	0.750	7.32	2.68	0.535	0.355	0.210	0.280
02	0.440	0.535	0.535	0.750	0.535	1.17	6.96	2.68	0.535	0.355	0.150	0.355
03	0.535	0.535	0.535	0.750	0.535	5.64	6.60	2.68	0.440	1.52	0.150	0.355
04	0.535	0.535	0.640	0.640	0.535	5.96	6.28	2.68	0.355	0.535	0.150	0.355
05	0.535	0.535	0.640	0.880	0.640	3.26	5.64	2.39	0.355	0.535	0.150	0.355
06	0.535	0.535	0.535	0.880	0.640	2.39	5.64	2.39	0.355	0.535	0.150	0.440
07	0.535	0.535	0.535	0.750	0.640	2.10	5.32	2.68	0.440	0.535	0.150	0.440
08	0.535	0.535	0.535	0.750	0.640	3.84	5.32	2.68	0.440	0.535	0.210	0.355
09	0.535	0.535	0.535	0.750	0.750	4.42	5.32	2.39	0.535	0.440	0.210	0.280
10	0.535	0.535	0.535	0.750	0.750	2.97	5.00	2.10	0.535	0.440	0.210	0.355
11	0.535	0.535	0.535	0.640	1.03	2.68	4.71	2.10	0.640	0.355	0.150	0.355
12	0.535	0.535	0.535	0.640	1.34	4.71	4.71	2.10	0.750	0.355	0.150	0.355
13	0.535	0.535	0.535	0.640	1.17	6.28	4.42	1.92	0.880	0.355	0.150	0.355
14	0.535	0.640	0.535	0.640	1.03	6.96	4.42	1.92	0.880	0.280	0.150	0.355
15	0.535	0.535	0.535	0.640	0.750	6.28	4.42	1.70	0.880	0.280	0.150	0.355
16	0.535	0.535	0.535	0.535	0.750	5.32	4.42	1.52	0.750	0.210	0.150	0.280
17	0.535	0.535	0.535	0.535	0.750	5.32	4.13	1.34	0.640	0.280	0.150	0.355
18	0.535	0.640	0.535	0.535	0.880	4.13	3.84	1.17	0.640	0.280	0.150	0.355
19	0.535	0.640	0.750	0.535	0.880	4.13	3.55	1.17	0.535	0.280	0.150	0.440
20	0.535	1.03	0.535	0.535	1.03	3.26	3.55	0.880	0.535	0.210	0.150	0.535
21	0.535	0.750	0.535	0.535	1.34	2.68	3.55	0.880	0.535	0.210	0.210	0.640
22	0.535	0.640	0.535	0.535	1.92	2.39	3.55	0.880	0.535	0.210	0.210	0.535
23	0.535	0.640	0.535	0.535	2.10	2.68	3.55	0.750	0.440	0.535	0.150	0.880
24	0.535	0.640	0.535	0.535	2.68	3.55	3.55	0.640	0.440	0.640	0.150	0.640
25	0.535	0.640	0.535	0.535	2.97	3.26	3.55	0.535	0.440	0.535	0.210	0.535
26	0.535	0.880	0.535	0.535	4.71	2.97	3.26	0.640	0.440	0.440	0.210	0.535
27	0.535	0.880	0.535	0.535	6.60	9.92	2.68	0.640	0.355	0.355	0.150	0.535
28	0.535	0.750	0.535	0.535	6.60	9.16	2.68	0.640	0.280	0.280	0.210	0.535
29	0.535	0.880	0.535	0.535	-----	8.78	2.68	0.535	0.280	0.210	0.210	0.535
30	0.535	0.750	0.535	0.535	-----	8.04	2.68	0.535	0.355	0.150	0.210	0.640
31	0.535	-----	0.750	0.535	-----	7.68	-----	0.535	-----	0.150	0.210	-----
Maks.	0.535	1.17	1.03	1.03	6.60	9.92	7.32	2.68	0.880	1.52	0.210	1.52
Min.	0.440	0.535	0.535	0.535	0.535	0.750	2.68	0.535	0.280	0.150	0.150	0.210
Ortalama	0.529	0.632	0.559	0.630	1.60	4.60	4.44	1.56	0.525	0.400	0.173	0.444
LT/SN/Km2	0.856	1.02	0.905	1.02	2.58	7.45	7.19	2.53	0.850	0.646	0.280	0.718
AKIM mm.	2.29	2.65	2.42	2.73	6.25	19.9	18.6	6.76	2.20	1.73	0.751	1.86
MİL. M3	1.42	1.64	1.50	1.69	3.86	12.3	11.5	4.18	1.36	1.07	0.464	1.15

SU YILI (2006) YILLIK TOPLAM AKIM 42.13 MİLYON M3 68 MM. 2.2 LT/SN/Km2

12. Sakarya Havzasi

D12A189 SÜVARİ ÇAYI ZEYDE

YERİ : **GÜDÜL-URUŞ NAHİYESİNDEN SONRA ZEYDE (DOĞANÇALI) KÖYÜNE VARILIR.KÖYÜN İÇİNDEKİ KÖPRÜNÜN 150 M.MEMBASINDADIR.**
32°5'55" Doğu - 40°17'40" Kuzey

YAĞIŞ ALANI : **190.60 km2** **YAKLAŞIK KOT : 854 m**

GÖZLEM SÜRESİ : **06.07.1986 - 30.09.2006**

ORTALAMA AKIMLAR : **Gözlem süresinde 1.923 m3/sn. (19 Yıllık) 2006 Su yılında 1.287 m3/sn.**

ANLIK EN ÇOK VE EN AZ AKIMLAR:

2006 Su yılında anlık ençok akım	**:**	**22.2**	**m3/sn**	**25.03.2006**
2006 Su yılında anlık enaz akım	**:**	**0.061**	**m3/sn**	**31.07.2006**
Gözlem süresinde anlık ençok akım	**:**	**57.0**	**m3/sn**	**08.04.1992**
Gözlem süresinde anlık enaz akım	**:**	**0.012**	**m3/sn**	**22.07.1990**

İstasyon için kullanılmış anahtar bulunamadı.

Akımlar 01 Ekim 2005 'den 30 Eylül 2006' a kadar m3/sn olarak

Gün	Ekim	Kasım	Aralık	Ocak	Şubat	Mart	Nisan	Mayıs	Haziran	Temmuz	Ağustos	Eylül
01	0.105	0.201	0.287	0.287	0.823	2.10	11.6	1.66	0.177	0.105	0.082	0.129
02	0.129	0.201	0.287	0.287	0.823	2.73	9.68	1.85	0.177	0.105	0.082	0.177
03	0.153	0.201	0.287	0.287	0.823	6.48	8.78	1.66	0.153	0.153	0.082	0.177
04	0.153	0.201	0.256	0.287	0.823	6.48	8.00	1.37	0.153	0.153	0.061	0.153
05	0.129	0.201	0.225	0.318	0.287	4.94	7.48	1.27	0.153	0.153	0.061	0.129
06	0.129	0.225	0.225	0.380	0.256	5.16	6.96	1.17	0.129	0.129	0.061	0.105
07	0.105	0.225	0.225	0.423	0.225	5.82	6.96	1.27	0.153	0.129	0.061	0.105
08	0.105	0.225	0.201	0.423	0.225	7.22	8.00	1.37	0.153	0.105	0.082	0.105
09	0.129	0.225	0.201	0.380	0.225	7.22	8.00	1.17	0.177	0.105	0.082	0.105
10	0.129	0.225	0.201	0.349	0.287	5.16	7.22	1.07	0.177	0.129	0.061	0.105
11	0.129	0.225	0.201	0.318	0.595	4.22	6.26	0.880	0.201	0.105	0.061	0.177
12	0.153	0.225	0.177	0.318	0.552	4.72	6.04	0.880	0.201	0.105	0.061	0.177
13	0.153	0.225	0.177	0.287	0.509	6.26	6.04	0.823	0.201	0.105	0.105	0.153
14	0.129	0.256	0.177	0.287	0.509	7.74	5.38	0.766	0.256	0.105	0.082	0.153
15	0.129	0.256	0.177	0.225	0.552	8.26	4.94	0.652	0.201	0.105	0.082	0.153
16	0.129	0.256	0.201	0.225	0.552	6.70	4.08	0.595	0.177	0.105	0.082	0.129
17	0.153	0.256	0.225	0.287	0.595	6.04	3.24	0.509	0.153	0.105	0.082	0.129
18	0.153	0.287	0.318	0.287	0.509	4.72	2.73	0.466	0.153	0.082	0.082	0.129
19	0.153	0.349	0.380	0.287	0.287	4.08	2.23	0.466	0.129	0.105	0.061	0.129
20	0.153	0.423	0.349	0.287	0.349	3.66	1.98	0.466	0.129	0.082	0.082	0.129
21	0.153	0.380	0.380	0.256	0.880	3.94	1.66	0.423	0.177	0.082	0.082	0.225
22	0.153	0.225	0.380	0.225	1.75	4.08	1.46	0.380	0.177	0.082	0.082	0.201
23	0.153	0.225	0.349	0.225	2.35	8.00	1.56	0.349	0.153	0.129	0.082	0.201
24	0.177	0.225	0.349	0.225	2.60	14.7	1.75	0.287	0.129	0.153	0.082	0.225
25	0.177	0.225	0.318	0.225	2.85	17.4	1.37	0.287	0.129	0.129	0.082	0.201
26	0.177	0.256	0.318	0.349	2.98	13.5	1.07	0.287	0.129	0.105	0.082	0.201
27	0.177	0.287	0.256	0.380	2.98	12.0	0.823	0.287	0.129	0.105	0.082	0.177
28	0.177	0.287	0.256	0.380	2.48	12.0	0.766	0.256	0.105	0.082	0.082	0.177
29	0.177	0.287	0.256	0.380	-----	11.2	0.709	0.256	0.129	0.082	0.082	0.201
30	0.177	0.287	0.287	0.595	-----	12.3	0.977	0.225	0.129	0.082	0.082	0.256
31	0.201	-----	0.318	0.766	-----	14.7	-----	0.225	-----	0.082	0.082	-----
Maks.	0.201	0.509	0.380	0.880	3.80	22.2	14.7	2.10	0.349	0.256	0.105	1.85
Min.	0.105	0.177	0.177	0.201	0.201	1.98	0.652	0.201	0.105	0.061	0.061	0.105
Ortalama	0.148	0.252	0.266	0.330	1.02	7.53	4.59	0.762	0.160	0.109	0.077	0.160
LT/SN/Km2	0.778	1.32	1.40	1.73	5.37	39.5	24.1	4.00	0.838	0.573	0.406	0.842
AKIM mm.	2.08	3.43	3.74	4.64	13.0	106.	62.4	10.7	2.17	1.53	1.09	2.18
MİL. M3	0.397	0.654	0.712	0.884	2.48	20.2	11.9	2.04	0.414	0.292	0.207	0.416

SU YILI (2006) YILLIK TOPLAM AKIM 40.60 MİLYON M3 213 MM. 6.8 LT/SN/Km2

12. Sakarya Havzasi

D12A192 ÇATÖREN BRJ. BRJ. ÇIKIŞI

YERİ : **ESKİŞEHİRDEN 43 KM SONRA SEYİTGAZİYE VARILIR SEYİTGAZİDENKIRKAYA GİDEN YOLUN 30 KM DE YOLUN ALTINDA BARAJIN 100MT**
30°34'0" Doğu - 39°19'0" Kuzey

YAĞIŞ ALANI : **712.00 km2** **YAKLAŞIK KOT : 2900 m**

GÖZLEM SÜRESİ : **01.12.1987 - 30.09.2006**

ORTALAMA AKIMLAR : **Gözlem süresinde 0.469 m3/sn. (15 Yıllık) 2006 Su yılında 0.700 m3/sn.**

ANLIK EN ÇOK VE EN AZ AKIMLAR:

2006 Su yılında anlık ençok akım	:	**5.80**	**m3/sn**	**29.07.2006**
2006 Su yılında anlık enaz akım	:	**0.000**	**m3/sn**	**01.10.2005**
Gözlem süresinde anlık ençok akım	:	**5.80**	**m3/sn**	**29.07.2006**
Gözlem süresinde anlık enaz akım	:	**0.000**	**m3/sn**	**01.10.1990**

Akımlar 01 Ekim 2005 'den 30 Eylül 2006' a kadar m3/sn olarak

Gün	Ekim	Kasım	Aralık	Ocak	Şubat	Mart	Nisan	Mayıs	Haziran	Temmuz	Ağustos	Eylül
01	KURU	KURU	KURU	KURU	KURU	KURU	KURU	0.600	0.380	2.70	5.80	4.00
02	KURU	KURU	KURU	KURU	KURU	KURU	KURU	0.600	0.380	2.70	5.80	4.00
03	KURU	KURU	KURU	KURU	KURU	KURU	KURU	0.600	0.380	2.70	5.40	4.00
04	KURU	KURU	KURU	KURU	KURU	KURU	KURU	0.600	0.380	2.70	4.60	3.20
05	KURU	KURU	KURU	KURU	KURU	KURU	KURU	0.600	0.290	2.50	4.00	1.55
06	KURU	KURU	KURU	KURU	KURU	KURU	KURU	0.600	0.037	2.00	4.20	0.600
07	KURU	KURU	KURU	KURU	KURU	KURU	KURU	0.600	0.037	2.00	3.90	0.135
08	KURU	KURU	KURU	KURU	KURU	KURU	KURU	0.600	0.037	2.20	3.90	0.135
09	KURU	KURU	KURU	KURU	KURU	KURU	KURU	0.600	0.037	2.50	4.00	0.135
10	KURU	KURU	KURU	KURU	KURU	KURU	KURU	0.600	0.037	2.50	4.00	0.135
11	KURU	KURU	KURU	KURU	KURU	KURU	KURU	1.25	0.840	2.50	3.30	0.135
12	KURU	KURU	KURU	KURU	KURU	KURU	KURU	1.85	1.85	2.50	0.210	0.135
13	KURU	KURU	KURU	KURU	KURU	KURU	KURU	1.85	1.85	2.50	0.135	0.135
14	KURU	KURU	KURU	KURU	KURU	KURU	KURU	1.85	1.85	2.50	0.135	0.135
15	KURU	KURU	KURU	KURU	KURU	KURU	KURU	1.85	1.10	2.50	0.135	0.135
16	KURU	KURU	KURU	KURU	KURU	KURU	KURU	1.85	0.078	2.50	0.135	0.135
17	KURU	KURU	KURU	KURU	KURU	KURU	KURU	1.85	1.40	2.50	0.135	0.135
18	KURU	KURU	KURU	KURU	KURU	KURU	KURU	1.85	2.30	2.50	0.135	0.135
19	KURU	KURU	KURU	KURU	KURU	KURU	KURU	1.85	2.70	2.50	0.135	0.135
20	KURU	KURU	KURU	KURU	KURU	KURU	KURU	1.85	2.70	2.50	0.135	0.135
21	KURU	KURU	KURU	KURU	KURU	KURU	0.078	1.85	2.90	2.50	0.135	0.135
22	KURU	KURU	KURU	KURU	KURU	KURU	0.210	1.85	2.90	2.50	0.135	0.135
23	KURU	KURU	KURU	KURU	KURU	KURU	0.210	0.078	2.90	2.50	0.135	0.135
24	KURU	KURU	KURU	KURU	KURU	KURU	0.135	0.078	2.90	2.50	0.135	0.135
25	KURU	KURU	KURU	KURU	KURU	KURU	0.078	0.078	3.00	3.70	0.135	0.135
26	KURU	KURU	KURU	KURU	KURU	KURU	0.078	0.078	3.00	4.80	0.135	0.135
27	KURU	KURU	KURU	KURU	KURU	KURU	0.078	0.078	2.70	4.80	0.135	0.135
28	KURU	KURU	KURU	KURU	KURU	KURU	0.078	0.078	2.70	4.80	1.10	0.135
29	KURU	KURU	KURU	KURU	-----	KURU	0.078	0.078	2.50	5.30	3.70	0.135
30	KURU	KURU	KURU	KURU	-----	KURU	0.290	0.135	2.50	5.80	4.00	0.135
31	KURU	-----	KURU	KURU	-----	KURU	-----	0.380	-----	5.80	4.00	-----
Maks.	KURU	KURU	KURU	KURU	KURU	KURU	0.290	1.85	3.00	5.80	5.80	4.00
Min.	KURU	KURU	KURU	KURU	KURU	KURU	KURU	0.078	0.037	2.00	0.135	0.135
Ortalama	KURU	KURU	KURU	KURU	KURU	KURU	0.044	0.925	1.56	3.05	2.06	0.686
LT/SN/Km2	0.000	0.000	0.000	0.000	0.000	0.000	0.061	1.30	2.18	4.28	2.90	0.964
AKIM mm.	0.000	0.000	0.000	0.000	0.000	0.000	0.159	3.48	5.66	11.5	7.76	2.50
MİL. M3	0.000	0.000	0.000	0.000	0.000	0.000	0.113	2.48	4.03	8.16	5.52	1.78

SU YILI (2006) YILLIK TOPLAM AKIM 22.08 MİLYON M3 31 MM. 1.0 LT/SN/Km2

12. Sakarya Havzasi

D12A193 BALIK BOGAZI D. KIRKA

YERİ : **ESKİŞEHİR-KIRKA KAZASININ ÇIKIŞINDAKİ KÖPRÜNÜN 50 MMANSABINDA SOL SAHİLDEDİR. 30°31'0" Doğu - 39°19'0" Kuzey**

YAĞIŞ ALANI : **685.00 km2** **YAKLAŞIK KOT : 1050 m**

GÖZLEM SÜRESİ : **01.12.1987 - 30.09.2006**

ORTALAMA AKIMLAR : **Gözlem süresinde 0.243 m3/sn. (11 Yıllık) 2006 Su yılında 0.126 m3/sn.**

ANLIK EN ÇOK VE EN AZ AKIMLAR:

2006 Su yılında anlık ençok akım	**:**	**1.86**	**m3/sn**	**03.03.2006**
2006 Su yılında anlık enaz akım	**:**	**0.000**	**m3/sn**	**10.07.2006**
Gözlem süresinde anlık ençok akım	**:**	**21.8**	**m3/sn**	**28.06.2004**
Gözlem süresinde anlık enaz akım	**:**	**0.000**	**m3/sn**	**01.10.1987**

Akımlar 01 Ekim 2005 'den 30 Eylül 2006' a kadar m3/sn olarak

Gün	Ekim	Kasım	Aralık	Ocak	Şubat	Mart	Nisan	Mayıs	Haziran	Temmuz	Ağustos	Eylül
01	0.017	0.062	0.062	0.017	0.094	1.50	0.094	0.094	0.016	0.007	0.002	0.002
02	0.036	0.062	0.036	0.062	0.094	1.27	0.094	0.094	0.016	0.007	KURU	0.007
03	0.036	0.062	0.036	0.036	0.094	1.86	0.094	0.094	0.016	0.016	KURU	0.007
04	0.036	0.062	0.036	0.036	0.094	1.15	0.094	0.094	0.016	0.007	0.002	0.007
05	0.036	0.062	0.036	0.036	0.094	0.798	0.094	0.094	0.016	0.007	KURU	0.007
06	0.036	0.062	0.036	0.036	0.094	0.623	0.094	0.094	0.033	0.007	KURU	0.007
07	0.036	0.062	0.036	0.062	0.094	0.564	0.094	0.094	0.033	0.007	KURU	0.007
08	0.036	0.062	0.036	0.062	0.094	0.564	0.094	0.130	0.033	0.007	0.002	0.007
09	0.036	0.062	0.036	0.094	0.094	0.681	0.094	0.094	0.033	0.007	0.002	0.007
10	0.036	0.094	0.036	0.094	0.094	0.623	0.094	0.094	0.033	KURU	0.002	0.007
11	0.036	0.094	0.036	0.094	0.220	0.623	0.094	0.094	0.033	KURU	KURU	0.002
12	0.036	0.094	0.036	0.094	0.270	0.623	0.094	0.094	0.033	KURU	0.002	0.002
13	0.036	0.094	0.062	0.094	0.389	0.623	0.094	0.094	0.033	KURU	0.002	0.002
14	0.036	0.094	0.062	0.094	0.447	0.681	0.094	0.094	0.033	0.002	0.002	0.002
15	0.036	0.130	0.036	0.094	0.447	0.681	0.094	0.094	0.033	0.002	0.002	0.007
16	0.036	0.036	0.036	0.094	0.447	0.564	0.094	0.080	0.033	KURU	0.002	0.007
17	0.036	0.036	0.017	0.094	0.447	0.564	0.094	0.051	0.016	0.002	0.002	0.007
18	0.036	0.036	0.036	0.094	0.740	0.506	0.094	0.051	0.016	0.002	0.002	0.007
19	0.036	0.062	0.036	0.094	0.740	0.447	0.094	0.051	0.033	0.002	KURU	0.007
20	0.036	0.036	0.036	0.094	0.740	0.330	0.062	0.051	0.033	0.002	0.002	0.007
21	0.036	0.062	0.036	0.094	0.915	0.270	0.062	0.051	0.033	0.002	KURU	0.007
22	0.036	0.036	0.036	0.094	1.03	0.270	0.062	0.051	0.033	0.002	KURU	0.007
23	0.036	0.062	0.036	0.094	0.974	0.220	0.094	0.033	0.033	0.002	KURU	0.007
24	0.036	0.062	0.036	0.094	0.974	0.220	0.094	0.033	0.033	0.002	KURU	0.016
25	0.036	0.062	0.036	0.094	1.44	0.220	0.094	0.033	0.033	0.007	KURU	0.016
26	0.062	0.062	0.036	0.094	1.68	0.220	0.094	0.033	0.033	0.002	0.002	0.016
27	0.062	0.062	0.036	0.094	1.56	0.170	0.094	0.033	0.033	0.002	0.002	0.016
28	0.062	0.062	0.062	0.094	1.21	0.170	0.094	0.033	0.033	0.002	KURU	0.016
29	0.062	0.062	0.036	0.094	-----	0.170	0.094	0.033	0.007	0.002	KURU	0.016
30	0.062	0.062	0.017	0.094	-----	0.130	0.094	0.016	0.007	0.002	KURU	0.016
31	0.062	-----	0.017	0.094	-----	0.130	-----	0.016	-----	0.002	0.002	-----
Maks.	0.062	0.130	0.062	0.094	1.68	1.86	0.094	0.130	0.033	0.016	0.002	0.016
Min.	0.017	0.036	0.017	0.017	0.094	0.130	0.062	0.016	0.007	KURU	KURU	0.002
Ortalama	0.040	0.065	0.038	0.081	0.558	0.563	0.091	0.068	0.027	0.004	0.001	0.008
LT/SN/Km2	0.059	0.095	0.055	0.118	0.814	0.822	0.133	0.099	0.040	0.005	0.002	0.012
AKIM mm.	0.158	0.247	0.147	0.316	1.97	2.20	0.344	0.264	0.103	0.014	0.004	0.031
MİL. M3	0.108	0.169	0.100	0.217	1.35	1.51	0.235	0.181	0.071	0.010	0.003	0.021

SU YILI (2006) YILLIK TOPLAM AKIM 3.97 MİLYON M3 6 MM. 0.2 LT/SN/Km2

12. Sakarya Havzasi

D12A194 HARAMİ D. KARAÖREN

YERİ : **ESKİŞEHİRDEN 43 KM SONRA SEYİTGAZİYE VARILIR .SEYİTGAZİDENKIRKAYA 7 KM SONRA KARAÖRENE VARILIR.İSTASYON KÖYE 3 KM**
30°34'0" Doğu - 39°14'0" Kuzey

YAĞIŞ ALANI : **712.00 km2** **YAKLAŞIK KOT : 1540 m**

GÖZLEM SÜRESİ : **01.12.1987 - 30.09.2006**

ORTALAMA AKIMLAR : **Gözlem süresinde 0.368 m3/sn. (16 Yıllık) 2006 Su yılında 0.276 m3/sn.**

ANLIK EN ÇOK VE EN AZ AKIMLAR:

2006 Su yılında anlık ençok akım	**:**	**4.34**	**m3/sn**	**27.02.2006**
2006 Su yılında anlık enaz akım	**:**	**0.000**	**m3/sn**	**29.07.2006**
Gözlem süresinde anlık ençok akım	**:**	**17.6**	**m3/sn**	**19.04.2002**
Gözlem süresinde anlık enaz akım	**:**	**0.000**	**m3/sn**	**01.10.1989**

Akımlar 01 Ekim 2005 'den 30 Eylül 2006' a kadar m3/sn olarak

Gün	Ekim	Kasım	Aralık	Ocak	Şubat	Mart	Nisan	Mayıs	Haziran	Temmuz	Ağustos	Eylül
01	0.011	0.026	0.048	0.048	0.076	3.14	0.504	0.210	0.115	0.048	KURU	0.160
02	0.011	0.026	0.048	0.048	0.076	2.42	0.504	0.210	0.115	0.048	KURU	0.210
03	0.026	0.026	0.048	0.048	0.076	3.26	0.504	0.210	0.115	0.270	KURU	0.076
04	0.026	0.048	0.048	0.048	0.076	2.54	0.426	0.210	0.115	0.048	KURU	0.048
05	0.026	0.048	0.048	0.048	0.076	1.82	0.348	0.210	0.076	0.048	KURU	0.048
06	0.026	0.048	0.048	0.048	0.076	1.37	0.348	0.210	0.076	0.048	KURU	0.048
07	0.026	0.048	0.048	0.048	0.076	1.26	0.270	0.504	0.076	0.048	KURU	0.048
08	0.026	0.048	0.048	0.048	0.076	1.26	0.270	0.758	0.076	0.048	KURU	0.048
09	0.026	0.048	0.048	0.048	0.076	1.59	0.270	0.504	0.076	0.048	KURU	0.048
10	0.026	0.048	0.048	0.048	0.076	1.48	0.270	0.210	0.076	0.048	0.001	0.048
11	0.026	0.048	0.048	0.048	0.076	1.59	0.270	0.160	0.115	0.026	0.001	0.048
12	0.026	0.048	0.048	0.048	0.076	1.94	0.270	0.160	0.115	0.026	0.001	0.004
13	0.026	0.048	0.048	0.048	0.076	1.82	0.270	0.160	0.115	0.026	0.004	KURU
14	0.026	0.048	0.048	0.048	0.076	1.94	0.270	0.160	0.115	0.026	0.004	KURU
15	0.026	0.048	0.048	0.048	0.076	2.06	0.270	0.160	0.115	0.026	0.004	KURU
16	0.026	0.048	0.048	0.048	0.076	1.48	0.270	0.210	0.115	0.011	0.011	KURU
17	0.026	0.048	0.048	0.048	0.076	1.48	0.270	0.210	0.115	0.011	0.011	KURU
18	0.026	0.048	0.048	0.048	0.270	1.37	0.270	0.160	0.115	0.004	0.011	KURU
19	0.026	0.048	0.048	0.048	1.05	1.26	0.210	0.160	0.076	0.004	0.048	KURU
20	0.026	0.048	0.048	0.048	1.94	0.954	0.210	0.160	0.076	0.001	0.048	KURU
21	0.026	0.048	0.048	0.076	2.30	0.856	0.210	0.160	0.076	0.004	0.048	KURU
22	0.026	0.048	0.048	0.076	3.38	0.660	0.210	0.160	0.076	0.004	0.048	KURU
23	0.026	0.048	0.048	0.076	3.38	0.582	0.210	0.160	0.076	0.001	0.048	KURU
24	0.026	0.048	0.048	0.076	3.26	0.582	0.210	0.115	0.076	0.001	0.048	KURU
25	0.026	0.048	0.048	0.076	3.62	0.758	0.210	0.115	0.076	0.001	0.048	KURU
26	0.026	0.048	0.048	0.076	3.98	0.582	0.210	0.115	0.048	0.001	0.048	KURU
27	0.026	0.048	0.048	0.076	4.34	0.582	0.210	0.115	0.026	0.026	0.048	KURU
28	0.026	0.048	0.076	0.076	3.74	0.582	0.210	0.115	0.048	0.001	0.048	KURU
29	0.026	0.048	0.115	0.076	-----	0.582	0.210	0.115	0.026	KURU	0.048	KURU
30	0.026	0.048	0.076	0.076	-----	0.504	0.210	0.115	0.115	KURU	0.048	0.011
31	0.026	-----	0.048	0.076	-----	0.504	-----	0.115	-----	KURU	0.076	-----
Maks.	0.026	0.048	0.115	0.076	4.34	3.26	0.504	0.758	0.115	0.270	0.076	0.210
Min.	0.011	0.026	0.048	0.048	0.076	0.504	0.210	0.115	0.026	KURU	KURU	KURU
Ortalama	0.025	0.046	0.052	0.058	1.16	1.38	0.280	0.204	0.088	0.029	0.023	0.028
LT/SN/Km2	0.035	0.064	0.073	0.081	1.63	1.94	0.393	0.287	0.123	0.041	0.032	0.040
AKIM mm.	0.094	0.167	0.195	0.218	3.95	5.19	1.02	0.769	0.319	0.109	0.085	0.103
MİL. M3	0.067	0.119	0.139	0.155	2.81	3.70	0.725	0.547	0.227	0.078	0.060	0.073

SU YILI (2006) YILLIK TOPLAM AKIM 8.70 MİLYON M3 12 MM. 0.4 LT/SN/Km2

12. Sakarya Havzasi

D12A197 DARIÇAYIR D. KARAPINAR

YERİ : **ADAPAZARI KARAPINAR KÖYÜ 32 KM. ASFALT KARAPINAR KÖYÜ-İSTASYON 2 KM.TARLA YOLU**
30°38'34" Doğu - 41°3'49" Kuzey

YAĞIŞ ALANI : **99.98 km2** **YAKLAŞIK KOT : 14.0780 m**

GÖZLEM SÜRESİ : **01.12.1988 - 30.09.2006**

ORTALAMA AKIMLAR : **Gözlem süresinde 2.765 m3/sn. (16 Yıllık) 2006 Su yılında 2.738 m3/sn.**

ANLIK EN ÇOK VE EN AZ AKIMLAR:

2006 Su yılında anlık ençok akım	**:**	**68.6**	**m3/sn**	**21.11.2005**
2006 Su yılında anlık enaz akım	**:**	**0.062**	**m3/sn**	**26.07.2006**
Gözlem süresinde anlık ençok akım	**:**	**84.0**	**m3/sn**	**14.08.1997**
Gözlem süresinde anlık enaz akım	**:**	**0.000**	**m3/sn**	**01.10.1988**

Akımlar 01 Ekim 2005 'den 30 Eylül 2006' a kadar m3/sn olarak

Gün	Ekim	Kasım	Aralık	Ocak	Şubat	Mart	Nisan	Mayıs	Haziran	Temmuz	Ağustos	Eylül
01	0.836	6.80	2.92	3.31	4.22	4.22	1.24	0.542	0.239	0.198	0.083	0.096
02	0.836	2.23	2.32	2.66	5.00	3.57	1.17	0.500	0.198	0.186	0.080	0.126
03	0.836	1.49	2.40	2.15	4.87	6.44	1.11	0.500	0.210	0.174	0.080	0.297
04	0.752	5.64	2.06	1.89	4.87	7.00	1.05	0.471	0.210	0.162	0.080	0.162
05	0.710	5.16	2.15	1.64	4.87	4.61	1.05	0.471	0.210	0.162	0.070	0.110
06	0.710	5.64	2.15	1.49	8.40	3.57	0.983	0.471	0.210	0.142	0.070	0.110
07	0.710	5.64	1.89	2.32	9.56	3.05	0.920	0.471	0.210	0.126	0.076	0.118
08	0.710	3.96	1.55	9.32	8.20	6.28	0.920	0.471	0.210	0.126	0.083	0.118
09	0.752	2.23	1.42	8.60	7.00	12.8	0.920	0.500	0.210	0.126	0.096	0.118
10	0.794	1.49	1.24	5.80	10.0	9.32	0.920	0.471	0.210	0.126	0.096	0.118
11	0.794	1.17	1.42	4.22	31.0	13.3	0.878	0.413	0.210	0.126	0.083	0.118
12	0.710	0.920	3.05	4.09	22.0	16.6	0.836	0.384	0.239	0.126	0.083	0.118
13	0.710	0.920	3.18	15.0	12.8	7.60	0.794	0.471	0.268	0.126	0.080	0.118
14	0.710	1.89	2.32	14.8	6.60	5.00	0.794	0.471	0.268	0.126	0.083	0.118
15	0.710	8.40	1.89	10.5	5.16	4.48	0.752	0.384	0.239	0.126	0.080	0.118
16	0.626	4.48	2.15	6.28	4.48	3.83	0.710	0.384	0.210	0.126	0.073	0.118
17	0.626	2.40	5.16	4.61	4.61	3.31	0.710	0.355	0.198	0.118	0.076	0.118
18	0.626	2.40	3.31	3.57	13.0	2.92	0.710	0.326	0.198	0.110	0.076	0.096
19	0.920	3.31	4.61	3.44	19.0	3.57	0.668	0.297	0.198	0.110	0.076	0.080
20	0.794	19.3	4.74	5.80	18.1	3.05	0.668	0.297	0.198	0.110	0.080	0.083
21	0.752	46.4	4.35	4.87	15.3	2.79	0.668	0.268	0.210	0.110	0.073	0.096
22	0.584	23.5	3.70	5.16	9.08	2.32	0.626	0.268	0.210	0.110	0.070	0.118
23	0.542	16.9	3.44	8.20	7.20	2.23	0.626	0.210	0.186	0.110	0.073	0.118
24	0.413	16.6	3.57	6.28	5.96	2.06	0.626	0.239	0.162	0.110	0.067	0.118
25	0.326	16.0	3.31	4.74	4.74	1.98	0.584	0.210	0.162	0.110	0.070	0.118
26	0.297	14.0	5.16	3.96	5.80	1.72	0.584	0.210	0.162	0.086	0.070	0.118
27	0.297	6.12	8.40	3.18	5.32	1.64	0.542	0.210	0.162	0.080	0.070	0.118
28	0.239	3.96	14.5	2.92	4.61	1.49	0.542	0.198	0.162	0.086	0.070	0.118
29	0.471	3.83	7.80	2.92	-----	1.49	0.542	0.198	0.186	0.086	0.070	0.118
30	7.60	3.83	4.35	3.05	-----	1.42	0.584	0.198	0.198	0.083	0.070	0.118
31	4.22	-----	3.70	3.57	-----	1.30	-----	0.268	-----	0.083	0.070	-----
Maks.	16.9	68.6	16.6	18.7	42.8	20.5	1.30	0.584	0.268	0.198	0.105	0.384
Min.	0.186	0.920	1.24	1.49	3.96	1.30	0.542	0.186	0.162	0.062	0.064	0.080
Ortalama	0.988	7.89	3.68	5.17	9.35	4.68	0.791	0.359	0.205	0.122	0.077	0.121
LT/SN/Km2	9.88	78.9	36.8	51.7	93.5	46.8	7.91	3.59	2.05	1.22	0.767	1.21
AKIM mm.	26.5	204.	98.7	139.	226.	125.	20.5	9.62	5.31	3.27	2.05	3.12
MİL. M3	2.64	20.4	9.87	13.9	22.6	12.5	2.05	0.961	0.531	0.327	0.205	0.312

SU YILI (2006) YILLIK TOPLAM AKIM 86.30 MİLYON M3 863 MM. 27.4 LT/SN/Km2

12. Sakarya Havzasi

D12A205 KAYI GÖLETİ DOLUSAVAK ÇIKIŞI

YERİ : **ESKİŞEHİRDEN 70 KM SONRA ÇİFTELERE VARILIP ORADAN 30 KMSİNDEERTEN KÖYÜNE KÖYÜN 3 KM BATISINDA İSTASYON.**
30°47'40" Doğu - 39°12'23" Kuzey

YAĞIŞ ALANI : **19.72 km2** **YAKLAŞIK KOT : 1155 m**

GÖZLEM SÜRESİ : **01.10.1989 - 30.09.2006**

ORTALAMA AKIMLAR : **Gözlem süresinde 0.027 m3/sn. (12 Yıllık) 2006 Su yılında 0.025 m3/sn.**

ANLIK EN ÇOK VE EN AZ AKIMLAR:

2006 Su yılında anlık ençok akım	**:**	**0.400 m3/sn**	**16.05.2006**
2006 Su yılında anlık enaz akım	**:**	**0.000 m3/sn**	**01.10.2005**
Gözlem süresinde anlık ençok akım	**:**	**6.20 m3/sn**	**26.03.1992**
Gözlem süresinde anlık enaz akım	**:**	**0.000 m3/sn**	**01.10.1989**

Akımlar 01 Ekim 2005 'den 30 Eylül 2006' a kadar m3/sn olarak

Gün	Ekim	Kasım	Aralık	Ocak	Şubat	Mart	Nisan	Mayıs	Haziran	Temmuz	Ağustos	Eylül
01	KURU	KURU	KURU	KURU	KURU	KURU	0.075	0.044	0.044	0.044	KURU	KURU
02	KURU	KURU	KURU	KURU	KURU	KURU	0.075	0.044	0.044	0.044	KURU	KURU
03	KURU	KURU	KURU	KURU	KURU	KURU	0.075	0.044	0.044	0.044	KURU	KURU
04	KURU	KURU	KURU	KURU	KURU	0.210	0.075	0.044	0.021	0.021	KURU	KURU
05	KURU	KURU	KURU	KURU	KURU	0.210	0.075	0.115	0.006	0.021	KURU	KURU
06	KURU	KURU	KURU	KURU	KURU	0.160	0.044	0.115	0.006	0.021	KURU	KURU
07	KURU	KURU	KURU	KURU	KURU	0.115	0.021	0.210	0.006	0.021	KURU	KURU
08	KURU	KURU	KURU	KURU	KURU	0.115	0.075	0.210	0.006	0.021	KURU	KURU
09	KURU	KURU	KURU	KURU	KURU	0.160	0.075	0.160	0.006	0.006	KURU	KURU
10	KURU	KURU	KURU	KURU	KURU	0.160	0.075	0.115	0.006	0.006	KURU	KURU
11	KURU	KURU	KURU	KURU	KURU	0.160	0.075	0.115	0.006	KURU	KURU	KURU
12	KURU	KURU	KURU	KURU	KURU	0.160	0.075	0.115	0.006	KURU	KURU	KURU
13	KURU	KURU	KURU	KURU	KURU	0.160	0.021	0.115	0.006	KURU	KURU	KURU
14	KURU	KURU	KURU	KURU	KURU	0.210	0.006	0.115	0.006	KURU	KURU	KURU
15	KURU	KURU	KURU	KURU	KURU	0.160	0.021	0.210	0.006	KURU	KURU	KURU
16	KURU	KURU	KURU	KURU	KURU	0.115	0.021	0.400	KURU	KURU	KURU	KURU
17	KURU	KURU	KURU	KURU	KURU	0.115	0.021	0.210	KURU	KURU	KURU	KURU
18	KURU	KURU	KURU	KURU	KURU	0.075	0.021	0.115	KURU	KURU	KURU	KURU
19	KURU	KURU	KURU	KURU	KURU	0.075	0.044	0.115	KURU	KURU	KURU	KURU
20	KURU	KURU	KURU	KURU	KURU	0.075	0.021	0.115	KURU	KURU	KURU	KURU
21	KURU	KURU	KURU	KURU	KURU	0.075	0.006	0.115	KURU	KURU	KURU	KURU
22	KURU	KURU	KURU	KURU	KURU	0.075	0.021	0.115	KURU	KURU	KURU	KURU
23	KURU	KURU	KURU	KURU	KURU	0.075	0.021	0.115	KURU	KURU	KURU	KURU
24	KURU	KURU	KURU	KURU	KURU	0.075	0.021	0.115	KURU	KURU	KURU	KURU
25	KURU	KURU	KURU	KURU	KURU	0.160	0.021	0.115	KURU	KURU	KURU	KURU
26	KURU	KURU	KURU	KURU	KURU	0.115	0.021	0.115	KURU	KURU	KURU	KURU
27	KURU	KURU	KURU	KURU	KURU	0.075	0.021	0.115	KURU	KURU	KURU	KURU
28	KURU	KURU	KURU	KURU	KURU	0.075	0.021	0.115	KURU	KURU	KURU	KURU
29	KURU	KURU	KURU	KURU	-----	0.075	0.021	0.115	0.115	KURU	KURU	KURU
30	KURU	KURU	KURU	KURU	-----	0.075	0.021	0.115	0.115	KURU	KURU	KURU
31	KURU	-----	KURU	KURU	-----	0.075	-----	0.075	-----	KURU	KURU	-----
Maks.	KURU	KURU	KURU	KURU	KURU	0.210	0.075	0.400	0.115	0.044	KURU	KURU
Min.	KURU	KURU	KURU	KURU	KURU	KURU	0.006	0.044	KURU	KURU	KURU	KURU
Ortalama	KURU	KURU	KURU	KURU	KURU	0.109	0.040	0.127	0.015	0.008	KURU	KURU
LT/SN/Km2	0.000	0.000	0.000	0.000	0.000	5.54	2.00	6.46	0.759	0.407	0.000	0.000
AKIM mm.	0.000	0.000	0.000	0.000	0.000	14.8	5.20	17.3	1.97	1.09	0.000	0.000
MİL. M3	0.000	0.000	0.000	0.000	0.000	0.292	0.102	0.341	0.039	0.022	0.000	0.000

SU YILI (2006) YILLIK TOPLAM AKIM 0.80 MİLYON M3 40 MM. 1.3 LT/SN/Km2

12. Sakarya Havzasi

D12A208 BUDAKLAR D. AKMEŞE

YERİ : İZMİT VİLAYETİNDEN AKMEŞE BELDESİNE GELİNİR. 8 KM SONRA BU-DAKLAR KÖYÜNE VARILIR
İSTASYON KÖYÜN 1 KM. MANSABINDA KÖPRÜDEDİRş
30°11'51" Doğu - 40°52'2" Kuzey

YAĞIŞ ALANI : 40,60 km2 **YAKLAŞIK KOT :** 79 m

GÖZLEM SÜRESİ : 05.03.1990 - 30.09.2006

ORTALAMA AKIMLAR : Gözlem süresinde 0.567 m3/sn. (11 Yıllık) 2006 Su yılında 0.544 m3/sn.

ANLIK EN ÇOK VE EN AZ AKIMLAR:

2006 Su yılında anlık ençok akım	:	26.5	m3/sn	20.11.2005
2006 Su yılında anlık enaz akım	:	0.024	m3/sn	04.06.2006
Gözlem süresinde anlık ençok akım	:	55.8	m3/sn	26.06.1999
Gözlem süresinde anlık enaz akım	:	0.024	m3/sn	23.07.1995

İstasyon için kullanılmış anahtar bulunamadı.

Akımlar 01 Ekim 2005 'den 30 Eylül 2006' a kadar m3/sn olarak

Gün	Ekim	Kasım	Aralık	Ocak	Şubat	Mart	Nisan	Mayıs	Haziran	Temmuz	Ağustos	Eylül
01	0.160	1.10	0.560	1.19	0.560	1.55	0.772	0.498	0.310	0.115	0.077	0.046
02	0.115	0.210	0.560	0.772	0.772	1.46	0.772	0.435	0.310	0.115	0.077	0.077
03	0.210	0.160	0.560	0.690	0.560	2.40	0.690	0.373	0.115	0.115	0.077	0.077
04	0.115	0.310	0.498	0.625	1.98	1.37	0.690	0.373	0.024	0.115	0.046	0.077
05	0.077	0.373	0.498	0.625	1.19	1.10	0.625	0.373	0.024	0.077	0.046	0.046
06	0.077	0.260	0.498	0.560	0.854	0.936	0.625	0.373	0.024	0.115	0.046	0.046
07	0.077	0.210	0.498	0.690	0.625	1.10	0.625	0.373	0.046	0.115	0.046	0.046
08	0.077	0.210	0.498	1.10	0.690	2.65	0.625	0.373	0.160	0.115	0.046	0.046
09	0.077	0.160	0.498	1.37	0.772	2.65	0.625	0.373	0.210	0.115	0.046	0.046
10	0.077	0.160	0.498	0.936	0.772	3.03	0.625	0.373	0.160	0.115	0.046	0.046
11	0.077	0.115	0.772	0.772	1.46	3.78	0.625	0.373	0.160	0.115	0.046	0.046
12	0.077	0.115	0.560	0.772	1.76	3.28	0.625	0.373	0.210	0.115	0.046	0.046
13	0.077	0.115	0.498	1.87	2.29	1.55	0.560	0.435	0.260	0.115	0.046	0.046
14	0.077	0.210	0.498	1.37	1.46	2.08	0.560	0.373	0.260	0.115	0.046	0.046
15	0.077	0.625	0.498	0.936	0.936	1.76	0.560	0.373	0.160	0.115	0.046	0.046
16	0.115	0.260	0.690	0.772	2.40	1.19	0.560	0.373	0.160	0.115	0.046	0.046
17	0.115	0.160	0.772	0.560	1.87	1.28	0.560	0.373	0.160	0.115	0.046	0.046
18	0.115	0.260	0.560	0.560	1.87	1.10	0.560	0.310	0.115	0.115	0.046	0.046
19	0.115	0.373	1.98	0.560	1.87	1.37	0.560	0.310	0.115	0.115	0.024	0.046
20	0.160	3.65	1.19	0.498	1.87	1.02	0.498	0.310	0.115	0.115	0.024	0.046
21	0.160	4.04	0.854	0.498	1.76	1.02	0.498	0.310	0.115	0.115	0.024	0.046
22	0.115	0.625	0.625	0.498	1.76	0.936	0.498	0.310	0.115	0.077	0.024	0.077
23	0.115	0.625	0.690	0.498	1.76	0.936	0.498	0.310	0.115	0.115	0.024	0.077
24	0.115	0.772	0.772	0.498	1.76	0.854	0.498	0.310	0.115	0.115	0.024	0.077
25	0.160	0.560	0.772	0.498	1.66	0.854	0.498	0.310	0.115	0.077	0.024	0.115
26	0.115	0.625	1.46	0.498	1.66	0.854	0.498	0.310	0.115	0.077	0.024	0.115
27	0.115	0.560	1.76	0.772	1.66	0.854	0.498	0.310	0.115	0.077	0.024	0.077
28	0.115	0.560	2.29	0.560	1.66	0.772	0.498	0.310	0.625	0.077	0.024	0.077
29	0.160	0.560	1.46	0.498	-----	0.772	0.498	0.310	0.160	0.077	0.024	0.077
30	0.435	0.560	0.936	0.498	-----	0.772	0.498	0.310	0.115	0.077	0.024	0.115
31	0.310	-----	2.40	0.498	-----	0.772	-----	0.310	-----	0.077	0.024	-----
Maks.	1.66	26.5	6.20	2.90	2.40	10.2	0.772	0.498	10.0	0.160	0.077	0.160
Min.	0.077	0.115	0.498	0.498	0.498	0.772	0.498	0.310	0.024	0.077	0.024	0.024
Ortalama	0.128	0.617	0.878	0.743	1.44	1.49	0.577	0.353	0.160	0.104	0.040	0.062
LT/SN/Km2	3.16	15.2	21.6	18.3	35.4	36.6	14.2	8.68	3.94	2.56	0.980	1.53
AKIM mm.	8.47	39.4	57.9	49.0	85.6	98.0	36.9	23.3	10.2	6.86	2.62	3.97
MİL. M3	0.344	1.60	2.35	1.99	3.48	3.98	1.50	0.944	0.415	0.278	0.107	0.161

SU YILI (2006) YILLIK TOPLAM AKIM 17.15 MİLYON M3 422 MM. 13.4 LT/SN/Km2

12. Sakarya Havzasi

D12A218 KOCA D. DOKUZOLUK

YERİ : **ADAPAZARI FERİZLİ İLÇESİNDEN 25 KM İLERDEKİ DOKUZOLUK KÖYÜNDEDİR. PAFTA: 25.000 EREĞ-F24-C3**
30°26'29" Doğu - 41°3'3" Kuzey

YAĞIŞ ALANI : **72,00 km2** **YAKLAŞIK KOT : 10 m**

GÖZLEM SÜRESİ : **24.10.1996 - 30.09.2006**

ORTALAMA AKIMLAR : **Gözlem süresinde 0.670 m3/sn. (10 Yıllık) 2006 Su yılında 0.750 m3/sn.**

ANLIK EN ÇOK VE EN AZ AKIMLAR:

2006 Su yılında anlık ençok akım	**:**	**12.9**	**m3/sn**	**20.11.2005**
2006 Su yılında anlık enaz akım	**:**	**0.000**	**m3/sn**	**08.10.2005**
Gözlem süresinde anlık ençok akım	**:**	**13.8**	**m3/sn**	**06.04.1997**
Gözlem süresinde anlık enaz akım	**:**	**0.000**	**m3/sn**	**07.08.1997**

1. Anahtar Eğrisi (Seviyeler cm olarak)

Seviye	Akım	Seviye	Akım	Seviye	Akım	Seviye	Akım
8	0.000	35	1.1	180	6.5	330	12.2
11	0.017	60	2.0	210	7.6	360	13.4
14	0.082	90	3.2	240	8.7	390	14.6
17	0.176	120	4.3	270	9.8	400	15.0
20	0.310	150	5.4	300	11.0		

Akımlar 01 Ekim 2005 'den 30 Eylül 2006' a kadar m3/sn olarak

Gün	Ekim	Kasım	Aralık	Ocak	Şubat	Mart	Nisan	Mayıs	Haziran	Temmuz	Ağustos	Eylül
01	0.001	2.64	0.900	0.850	2.79	1.05	0.465	0.255	0.052	0.017	KURU	KURU
02	0.001	0.255	0.737	0.737	3.94	0.900	0.465	0.255	0.052	0.007	KURU	KURU
03	0.003	0.176	0.950	0.624	3.27	2.49	0.465	0.255	0.082	0.007	KURU	KURU
04	0.001	0.111	0.900	0.516	3.09	1.10	0.465	0.255	0.052	0.007	KURU	KURU
05	0.001	0.362	0.794	0.516	2.90	1.05	0.465	0.220	0.052	0.007	KURU	KURU
06	0.001	0.465	0.737	0.465	4.38	0.900	0.465	0.176	0.052	0.007	KURU	KURU
07	0.001	0.465	0.681	1.43	3.27	0.950	0.465	0.176	0.052	0.007	KURU	KURU
08	KURU	0.310	0.681	3.86	3.64	3.57	0.465	0.145	0.052	0.003	KURU	KURU
09	KURU	0.220	0.681	2.79	3.27	5.05	0.465	0.176	0.052	0.003	KURU	KURU
10	KURU	0.176	0.681	1.14	3.83	1.50	0.516	0.145	0.082	0.003	KURU	KURU
11	KURU	0.176	1.05	1.00	6.60	0.950	0.413	0.145	0.052	0.003	KURU	KURU
12	KURU	0.145	0.950	1.43	3.75	0.900	0.465	0.176	0.052	0.003	KURU	KURU
13	0.001	0.145	0.794	1.83	3.64	0.737	0.413	0.220	0.082	0.003	KURU	KURU
14	0.001	0.516	0.737	1.10	3.09	0.794	0.413	0.176	0.145	0.003	KURU	KURU
15	0.001	4.16	0.737	0.950	2.75	0.950	0.362	0.176	0.082	0.001	KURU	KURU
16	0.001	0.413	0.900	0.900	2.68	1.05	0.310	0.176	0.082	0.001	KURU	KURU
17	0.017	0.310	1.19	0.794	2.64	0.950	0.255	0.176	0.052	KURU	KURU	KURU
18	0.007	0.413	0.900	0.794	3.83	0.850	0.255	0.145	0.052	KURU	KURU	KURU
19	0.017	0.568	9.23	1.90	2.24	1.00	0.255	0.111	0.034	KURU	KURU	KURU
20	0.017	5.64	3.09	6.12	1.43	0.850	0.255	0.111	0.034	0.001	KURU	KURU
21	0.007	10.7	1.36	3.42	0.900	0.737	0.255	0.111	0.034	0.001	KURU	KURU
22	0.007	2.12	1.14	2.42	0.900	0.681	0.255	0.111	0.034	KURU	KURU	KURU
23	0.007	1.28	1.46	2.49	0.850	0.624	0.255	0.111	0.017	KURU	KURU	KURU
24	0.007	5.08	2.27	1.83	0.850	0.624	0.255	0.111	0.017	KURU	KURU	KURU
25	0.007	2.09	2.01	1.64	0.794	0.624	0.255	0.082	0.034	KURU	KURU	KURU
26	0.007	5.27	2.90	2.57	1.23	0.568	0.255	0.111	0.034	KURU	KURU	0.003
27	0.007	1.36	1.32	2.35	1.32	0.568	0.255	0.111	0.017	KURU	KURU	0.003
28	0.007	1.14	1.00	2.20	0.900	0.516	0.255	0.082	0.681	KURU	KURU	0.003
29	0.007	1.05	0.900	1.94	-----	0.516	0.255	0.082	0.176	KURU	KURU	0.003
30	0.681	1.00	0.850	1.36	-----	0.465	0.255	0.082	0.034	KURU	KURU	0.007
31	0.737	-----	0.950	1.50	-----	0.465	-----	0.111	-----	KURU	KURU	-----
Maks.	2.49	12.9	12.6	7.34	11.8	6.64	0.516	0.310	2.38	0.034	KURU	0.034
Min.	KURU	0.111	0.681	0.465	0.737	0.465	0.220	0.082	0.017	KURU	KURU	KURU
Ortalama	0.050	1.63	1.40	1.72	2.67	1.10	0.355	0.154	0.078	0.003	KURU	0.001
LT/SN/Km2	0.695	22.6	19.5	24.0	37.1	15.2	4.93	2.14	1.08	0.038	0.000	0.009
AKIM mm.	1.86	58.5	52.2	64.2	89.7	40.8	12.8	5.73	2.79	0.101	0.000	0.023
MİL. M3	0.134	4.21	3.76	4.62	6.46	2.94	0.920	0.413	0.201	0.007	0.000	0.002

SU YILI (2006) YILLIK TOPLAM AKIM 23.67 MİLYON M3 329 MM. 10.4 LT/SN/Km2

12. Sakarya Havzasi

D12A219 ANADERE ŞAHTIMARI

YERİ : **ADAPAZARI KAYNARCA İLÇESİNE GİRMEDEN İLK KÖPRÜDEN SOLA DÖNÜLÜR. İSTASYON KÖPRÜDEN 3 KM İLERİSİNDEDİR. PAFTA: 25.000 EREĞ-F24-C4**
30°15'45" Doğu - 41°0'17" Kuzey

YAĞIŞ ALANI : **70,10 km2** **YAKLAŞIK KOT : 52 m**

GÖZLEM SÜRESİ : **25.10.1996 - 30.09.2006**

ORTALAMA AKIMLAR : **Gözlem süresinde 0.890 m3/sn. (10 Yıllık) 2006 Su yılında 1.005 m3/sn.**

ANLIK EN ÇOK VE EN AZ AKIMLAR:

2006 Su yılında anlık ençok akım	**:**	**17.1**	**m3/sn**	**11.02.2006**
2006 Su yılında anlık enaz akım	**:**	**0.000**	**m3/sn**	**02.10.2005**
Gözlem süresinde anlık ençok akım	**:**	**26.3**	**m3/sn**	**08.02.2003**
Gözlem süresinde anlık enaz akım	**:**	**0.000**	**m3/sn**	**07.08.1997**

İstasyon için kullanılmış anahtar bulunamadı.

Akımlar 01 Ekim 2005 'den 30 Eylül 2006' a kadar m3/sn olarak

Gün	Ekim	Kasım	Aralık	Ocak	Şubat	Mart	Nisan	Mayıs	Haziran	Temmuz	Ağustos	Eylül
01	0.001	0.668	0.980	1.66	2.42	1.80	0.782	0.360	0.110	0.270	0.110	0.150
02	KURU	0.240	0.980	1.47	3.12	1.37	0.782	0.310	0.150	0.270	0.110	0.110
03	KURU	0.354	1.47	1.38	3.22	3.78	0.782	0.270	0.110	0.270	0.110	0.150
04	KURU	0.295	1.30	1.38	3.32	1.71	0.782	0.270	0.110	0.310	0.110	0.110
05	0.001	0.824	1.14	1.30	3.32	1.45	0.782	0.230	0.110	0.270	0.110	0.110
06	0.007	0.590	1.06	1.30	7.63	1.19	0.708	0.190	0.110	0.270	0.150	0.110
07	0.007	0.531	0.980	1.76	3.96	1.28	0.708	0.190	0.150	0.270	0.150	0.071
08	0.007	0.824	0.980	2.23	5.24	3.78	0.708	0.190	0.230	0.230	0.230	0.071
09	0.007	0.590	0.980	2.23	4.92	5.43	0.782	0.190	0.360	0.230	0.190	0.071
10	0.007	0.413	1.06	1.85	7.19	3.34	0.782	0.150	0.410	0.230	0.230	0.071
11	0.007	0.354	1.57	1.76	9.37	2.68	0.708	0.150	0.360	0.230	0.150	0.042
12	0.001	0.354	1.30	1.66	3.89	2.57	0.708	0.150	0.310	0.230	0.110	0.042
13	0.001	0.354	1.22	2.04	3.67	1.80	0.708	0.190	0.410	0.230	0.110	0.042
14	0.007	0.531	1.22	1.94	2.90	2.35	0.708	0.150	0.410	0.230	0.150	0.042
15	0.001	2.04	1.22	1.66	2.24	2.46	0.782	0.150	0.360	0.190	0.110	0.042
16	0.001	0.824	1.14	1.57	2.02	1.80	0.708	0.150	0.360	0.190	0.110	0.020
17	0.007	0.531	2.23	1.47	2.35	1.71	0.634	0.150	0.360	0.190	0.150	0.020
18	0.032	0.746	1.38	1.47	4.88	1.63	0.510	0.110	0.310	0.230	0.150	0.020
19	0.032	0.824	8.39	2.42	3.34	1.91	0.460	0.110	0.310	0.190	0.110	0.020
20	0.007	9.37	3.32	4.06	2.57	1.45	0.460	0.110	0.270	0.150	0.110	0.020
21	0.007	6.32	2.62	2.62	1.91	1.28	0.460	0.110	0.310	0.150	0.150	0.020
22	0.032	3.32	2.04	2.32	1.63	1.28	0.410	0.110	0.270	0.150	0.110	0.020
23	0.032	2.23	2.72	2.42	1.45	1.28	0.460	0.110	0.310	0.190	0.110	0.020
24	0.032	3.32	2.72	2.32	1.37	1.28	0.410	0.110	0.310	0.190	0.071	0.009
25	0.032	2.32	2.42	2.42	1.37	1.28	0.410	0.110	0.230	0.150	0.071	0.009
26	0.032	3.32	2.82	2.52	1.80	1.19	0.410	0.110	0.270	0.150	0.110	0.020
27	0.032	1.76	2.42	2.52	1.71	1.10	0.410	0.110	0.270	0.110	0.110	0.020
28	0.032	1.30	2.13	2.52	1.63	1.02	0.360	0.110	0.360	0.150	0.150	0.009
29	0.007	1.14	1.94	2.52	-----	1.19	0.360	0.110	0.310	0.110	0.110	0.009
30	0.007	1.06	1.66	2.32	-----	1.10	0.410	0.110	0.270	0.110	0.110	0.009
31	0.007	-----	2.13	2.32	-----	1.02	-----	0.150	-----	0.110	0.110	-----
Maks.	0.062	11.8	11.1	6.65	17.1	7.85	0.856	0.410	1.37	0.360	0.270	0.270
Min.	KURU	0.240	0.902	1.30	1.37	0.930	0.360	0.071	0.071	0.071	0.071	0.001
Ortalama	0.012	1.58	1.92	2.05	3.37	1.89	0.603	0.162	0.274	0.202	0.128	0.049
LT/SN/Km2	0.177	22.5	27.4	29.2	48.1	26.9	8.60	2.31	3.91	2.88	1.83	0.703
AKIM mm.	0.475	58.4	73.4	78.2	116.	72.1	22.3	6.19	10.1	7.70	4.90	1.82
MİL. M3	0.033	4.09	5.14	5.48	8.16	5.06	1.56	0.434	0.710	0.540	0.343	0.128

SU YILI (2006) YILLIK TOPLAM AKIM 31.68 MİLYON M3 452 MM. 14.3 LT/SN/Km2

12. Sakarya Havzasi

D12A224 AKMEŞE D. DEREKÖY

YERİ : **ADAPAZARI KAYNARCA KARAYOLUNUN 18. KM SONRASINDAKİ KAYRANCA KÖYÜNDEN 5 KM İLERDEKİ DEREKÖY MEVKİİNDEDİR. PAFTA: 25.000 ADA-G24-B1 30°18'48" Doğu - 40°53'37" Kuzey**

YAĞIŞ ALANI : **111,10 km2** **YAKLAŞIK KOT : 30 m**

GÖZLEM SÜRESİ : **10.07.1997 - 30.09.2006**

ORTALAMA AKIMLAR : **Gözlem süresinde 1.301 m3/sn. (9 Yıllık) 2006 Su yılında 1.480 m3/sn.**

ANLIK EN ÇOK VE EN AZ AKIMLAR:

2006 Su yılında anlık ençok akım	:	**71.0**	**m3/sn**	**11.02.2006**
2006 Su yılında anlık enaz akım	:	**0.000**	**m3/sn**	**29.07.2006**
Gözlem süresinde anlık ençok akım	:	**104.**	**m3/sn**	**08.01.2000**
Gözlem süresinde anlık enaz akım	:	**0.000**	**m3/sn**	**30.06.2001**

İstasyon için kullanılmış anahtar bulunamadı.

Akımlar 01 Ekim 2005 'den 30 Eylül 2006' a kadar m3/sn olarak

Gün	Ekim	Kasım	Aralık	Ocak	Şubat	Mart	Nisan	Mayıs	Haziran	Temmuz	Ağustos	Eylül
01	0.147	4.80	0.890	3.00	3.80	2.66	1.14	0.562	0.147	0.220	KURU	0.007
02	0.074	0.562	0.808	2.15	5.42	1.81	1.14	0.480	0.111	0.220	KURU	0.074
03	0.324	0.324	1.47	1.81	4.80	6.89	1.14	0.480	0.111	0.220	KURU	0.147
04	0.184	0.272	1.14	1.64	4.40	3.00	1.05	0.480	0.074	0.220	KURU	0.074
05	0.074	1.14	1.05	1.47	4.00	1.98	1.05	0.562	0.074	0.184	0.003	0.038
06	0.038	0.726	0.890	1.47	9.66	1.47	1.05	0.480	0.074	0.147	0.001	0.038
07	0.017	0.562	0.808	1.81	5.84	1.81	0.972	0.480	0.111	0.111	KURU	0.038
08	0.017	0.324	0.726	3.40	8.25	7.33	0.972	0.428	0.147	0.111	KURU	0.038
09	0.038	0.220	0.808	4.00	7.33	12.3	0.972	0.428	0.220	0.111	KURU	0.017
10	0.017	0.184	0.726	2.49	12.0	6.26	0.972	0.428	0.324	0.147	KURU	0.017
11	0.017	0.147	1.22	2.32	34.0	5.84	0.972	0.376	0.272	0.184	KURU	0.017
12	0.038	0.147	1.22	2.49	6.89	6.47	0.890	0.376	0.220	0.074	KURU	0.038
13	0.038	0.147	0.972	6.26	6.68	3.60	0.890	0.644	0.324	0.074	KURU	0.017
14	0.038	0.644	0.808	3.40	4.60	4.20	0.808	0.480	0.808	0.074	KURU	0.017
15	0.038	1.64	0.808	2.66	3.40	4.80	0.808	0.428	0.376	0.038	KURU	0.017
16	0.111	0.562	1.14	2.15	2.83	2.83	0.808	0.480	0.324	0.017	KURU	0.017
17	0.184	0.376	2.32	1.81	2.83	3.00	0.808	0.428	0.272	0.074	KURU	0.017
18	0.147	0.808	1.22	1.64	6.26	2.49	0.808	0.428	0.220	0.111	KURU	0.017
19	0.111	1.14	11.0	4.40	5.84	3.20	0.808	0.376	0.220	0.074	KURU	0.007
20	0.147	5.21	5.00	8.25	5.21	2.32	0.726	0.376	0.220	0.038	KURU	0.017
21	0.220	19.3	3.20	4.00	3.60	1.98	0.726	0.376	0.220	0.017	KURU	0.017
22	0.111	2.15	2.15	3.40	2.49	1.81	0.726	0.324	0.184	0.017	KURU	0.038
23	0.074	1.47	2.66	4.00	2.15	1.64	0.726	0.272	0.147	0.007	KURU	0.038
24	0.038	3.00	3.60	3.00	1.81	1.64	0.726	0.272	0.111	0.003	KURU	0.074
25	0.074	1.81	3.20	3.00	1.64	1.64	0.726	0.220	0.038	KURU	KURU	0.111
26	0.074	2.32	3.60	3.60	2.49	1.47	0.562	0.272	0.074	KURU	KURU	0.147
27	0.074	1.30	4.00	3.40	3.20	1.30	0.562	0.272	0.038	KURU	KURU	0.147
28	0.074	1.14	4.60	3.40	2.66	1.22	0.562	0.220	1.47	KURU	KURU	0.074
29	0.074	1.05	3.40	3.00	-----	1.30	0.562	0.220	0.562	KURU	KURU	0.074
30	0.644	1.05	2.32	2.66	-----	1.22	0.562	0.184	0.272	KURU	0.007	0.147
31	0.726	-----	5.21	2.83	-----	1.14	-----	0.184	-----	KURU	0.007	-----
Maks.	1.81	53.6	15.5	19.6	71.0	15.2	1.14	0.890	13.1	0.272	0.017	0.184
Min.	0.017	0.147	0.726	1.30	1.64	1.14	0.562	0.184	0.017	KURU	KURU	0.007
Ortalama	0.128	1.82	2.35	3.06	5.86	3.25	0.841	0.388	0.259	0.080	0.001	0.051
LT/SN/Km2	1.16	16.4	21.2	27.6	52.7	29.2	7.57	3.49	2.33	0.724	0.005	0.461
AKIM mm.	3.10	42.4	56.7	73.8	128.	78.2	19.6	9.34	6.04	1.94	0.014	1.19
MİL. M3	0.344	4.71	6.30	8.20	14.2	8.69	2.18	1.04	0.671	0.215	0.002	0.133

SU YILI (2006) YILLIK TOPLAM AKIM 46.68 MİLYON M3 420 MM. 13.3 LT/SN/Km2

12. Sakarya Havzasi

D12A225 DEĞİRMENDERE GÜNDÜZLER

YERİ : ESKISEHIR-CAVLUM YOLUNDAN SOLA SAPILARAK GUNDUZLER KOYUNE VARILIR. ISTASYON 500 M. KUZEYDEDIR.
30°47'0" Doğu - 39°53'0" Kuzey

YAĞIŞ ALANI : 21.00 km2 **YAKLAŞIK KOT :** 860 m

GÖZLEM SÜRESİ : 01.10.1997 - 30.09.2006

ORTALAMA AKIMLAR : Gözlem süresinde 0.133 m3/sn. (9 Yıllık) 2006 Su yılında 0.125 m3/sn.

ANLIK EN ÇOK VE EN AZ AKIMLAR:

2006 Su yılında anlık ençok akım	:	2.02	m3/sn	14.03.2006
2006 Su yılında anlık enaz akım	:	0.000	m3/sn	16.04.2006
Gözlem süresinde anlık ençok akım	:	3.70	m3/sn	25.12.2001
Gözlem süresinde anlık enaz akım	:	0.000	m3/sn	06.10.2001

1. Anahtar Eğrisi (Seviyeler cm olarak)

Seviye	Akım	Seviye	Akım	Seviye	Akım	Seviye	Akım
1	0.000	11	0.048	61	1.3	111	3.7
3	0.003	21	0.202	71	1.7	121	4.4
5	0.009	31	0.411	81	2.2	131	5.0
7	0.018	41	0.654	91	2.6	141	5.8
9	0.031	51	0.941	101	3.0	151	6.7

Akımlar 01 Ekim 2005 'den 30 Eylül 2006' a kadar m3/sn olarak

Gün	Ekim	Kasım	Aralık	Ocak	Şubat	Mart	Nisan	Mayıs	Haziran	Temmuz	Ağustos	Eylül
01	0.039	0.005	0.018	0.286	0.202	1.11	0.202	0.018	0.048	0.005	0.113	0.005
02	0.039	0.005	0.018	0.265	0.202	1.04	0.184	0.018	0.074	0.005	0.024	0.005
03	0.031	0.005	0.018	0.244	0.202	1.49	0.184	0.018	0.024	0.009	0.024	0.005
04	0.031	0.005	0.018	0.223	0.202	1.04	0.166	0.024	0.031	0.005	0.100	0.005
05	0.024	0.005	0.018	0.348	0.087	0.826	0.149	0.031	0.018	0.024	0.005	0.005
06	0.024	0.013	0.018	0.369	0.087	0.711	0.131	0.024	0.131	0.031	0.005	0.005
07	0.024	0.024	0.018	0.348	0.087	0.740	0.113	0.024	0.149	0.018	0.002	0.005
08	0.018	0.018	0.018	0.286	0.087	0.941	0.087	0.024	0.018	0.013	0.009	0.005
09	0.018	0.013	0.018	0.265	0.074	0.884	0.100	0.024	0.002	0.009	0.024	0.005
10	0.018	0.013	0.018	0.223	0.074	0.769	0.074	0.024	0.002	0.005	0.031	0.005
11	0.018	0.013	0.018	0.184	0.074	0.740	0.061	0.024	0.002	0.005	0.009	0.005
12	0.018	0.013	0.018	0.166	0.048	0.974	0.048	0.018	0.013	0.005	0.005	0.005
13	0.018	0.013	0.018	0.149	0.061	1.11	0.061	0.031	0.074	0.005	0.018	0.005
14	0.018	0.013	0.018	0.131	0.074	1.27	0.018	0.024	0.024	0.005	0.018	0.005
15	0.018	0.013	0.018	0.113	0.131	1.04	0.018	0.024	0.024	0.005	0.002	0.005
16	0.018	0.018	0.061	0.113	0.149	0.826	0.013	0.024	0.013	0.005	0.005	0.005
17	0.018	0.018	0.061	0.100	0.149	0.683	0.013	0.024	0.018	0.005	0.009	0.005
18	0.024	0.018	0.061	0.087	0.131	0.581	0.013	0.024	0.018	0.005	0.002	0.005
19	0.031	0.018	0.061	0.100	0.100	0.557	0.024	0.024	0.009	0.005	0.002	0.005
20	0.031	0.018	0.074	0.087	0.184	0.508	0.024	0.024	0.005	0.005	0.005	0.005
21	0.031	0.018	0.074	0.087	0.327	0.533	0.024	0.024	0.013	0.024	0.005	0.009
22	0.039	0.018	0.074	0.087	0.460	0.557	0.018	0.039	0.031	0.087	0.002	0.009
23	0.048	0.018	0.074	0.074	0.654	0.683	0.018	0.024	0.018	0.031	0.002	0.005
24	0.074	0.018	0.074	0.074	0.826	0.711	0.018	0.100	0.009	0.005	0.002	0.005
25	0.074	0.018	0.074	0.074	0.941	0.557	0.024	0.100	0.039	0.002	0.002	0.005
26	0.018	0.018	0.074	0.074	1.14	0.460	0.024	0.265	0.005	0.002	0.002	0.005
27	0.005	0.018	0.074	0.074	1.01	0.390	0.024	0.286	0.005	0.002	0.002	0.009
28	0.005	0.018	0.074	0.074	0.884	0.327	0.018	0.149	0.005	0.002	0.013	0.009
29	0.005	0.018	0.131	0.202	-----	0.286	0.018	0.286	0.005	0.031	0.009	0.009
30	0.005	0.018	0.223	0.202	-----	0.244	0.018	0.013	0.009	0.100	0.002	0.005
31	0.005	-----	0.265	0.202	-----	0.223	-----	0.048	-----	0.048	0.002	-----
Maks.	0.074	0.184	0.265	0.508	1.61	2.02	0.390	1.14	1.07	0.533	0.411	0.061
Min.	0.005	0.005	0.018	0.074	0.048	0.202	KURU	0.013	KURU	KURU	KURU	0.002
Ortalama	0.025	0.015	0.058	0.171	0.309	0.736	0.063	0.058	0.028	0.016	0.015	0.006
LT/SN/Km2	1.21	0.700	2.76	8.16	14.7	35.0	3.00	2.77	1.33	0.780	0.699	0.270
AKIM mm.	3.24	1.81	7.40	21.9	35.6	93.9	7.76	7.42	3.44	2.09	1.87	0.699
MİL. M3	0.068	0.038	0.155	0.459	0.747	1.97	0.163	0.156	0.072	0.044	0.039	0.015

SU YILI (2006) YILLIK TOPLAM AKIM 3.93 MİLYON M3 187 MM. 5.9 LT/SN/Km2

12. Sakarya Havzasi

D12A227 ÇARSAMBA D. HİSARCIK

YERİ : **ESK VE İST. UZAKLIĞI 40 KM. ESK. 'DEN KESKİN KÖYÜNE ORADAN EĞRİGÖZ,ULUDERE,ORTACAYA GİDİLİR.ORTACA KÖYÜNE UZAKLIĞI 6 KMDİR.SERVİS YOLUNA UZAKLIĞI 1.5 KMDİR 30°19'0" Doğu - 39°59'0" Kuzey**

YAĞIŞ ALANI : **23.32 km2** **YAKLAŞIK KOT : 900 m**

GÖZLEM SÜRESİ : **01.10.1997 - 30.09.2006**

ORTALAMA AKIMLAR : **Gözlem süresinde 0.239 m3/sn. (10 Yıllık) 2006 Su yılında 0.246 m3/sn.**

ANLIK EN ÇOK VE EN AZ AKIMLAR:

2006 Su yılında anlık ençok akım	:	**2.96**	**m3/sn**	**20.02.2006**
2006 Su yılında anlık enaz akım	:	**0.003**	**m3/sn**	**03.07.2006**
Gözlem süresinde anlık ençok akım	:	**4.37**	**m3/sn**	**26.12.2001**
Gözlem süresinde anlık enaz akım	:	**0.000**	**m3/sn**	**02.09.2002**

Akımlar 01 Ekim 2005 'den 30 Eylül 2006' a kadar m3/sn olarak

Gün	Ekim	Kasım	Aralık	Ocak	Şubat	Mart	Nisan	Mayıs	Haziran	Temmuz	Ağustos	Eylül
01	0.009	0.017	0.060	0.166	0.166	1.17	1.17	0.090	0.122	0.090	0.017	0.017
02	0.009	0.017	0.122	0.166	0.166	1.30	1.17	0.090	0.122	0.090	0.017	0.017
03	0.009	0.017	0.090	0.166	0.166	1.43	1.17	0.090	0.122	0.045	0.017	0.009
04	0.009	0.017	0.090	0.166	0.166	1.43	1.17	0.090	0.122	0.037	0.017	0.009
05	0.009	0.017	0.122	0.166	0.166	1.43	1.17	0.090	0.122	0.037	0.017	0.009
06	0.009	0.029	0.122	0.211	0.166	1.43	1.12	0.090	0.122	0.037	0.017	0.009
07	0.009	0.029	0.090	0.211	0.166	1.43	0.444	0.090	0.122	0.037	0.017	0.009
08	0.009	0.017	0.090	0.211	0.166	1.43	0.150	0.090	0.122	0.037	0.017	0.009
09	0.009	0.017	0.090	0.211	0.166	1.43	0.150	0.090	0.122	0.037	0.017	0.009
10	0.009	0.017	0.090	0.211	0.166	1.43	0.150	0.090	0.122	0.017	0.017	0.009
11	0.009	0.017	0.090	0.211	0.469	1.43	0.150	0.166	0.122	0.017	0.017	0.009
12	0.009	0.017	0.090	0.211	0.537	1.30	0.150	0.122	0.060	0.017	0.017	0.009
13	0.009	0.017	0.090	0.211	0.537	1.30	0.150	0.122	0.090	0.017	0.017	0.009
14	0.009	0.029	0.090	0.211	0.537	1.30	0.150	0.122	0.120	0.017	0.017	0.009
15	0.009	0.029	0.090	0.166	0.537	1.30	0.150	0.122	0.120	0.017	0.017	0.009
16	0.009	0.029	0.090	0.166	0.402	1.30	0.120	0.122	0.120	0.017	0.017	0.009
17	0.009	0.029	0.090	0.166	0.334	1.30	0.120	0.122	0.120	0.017	0.017	0.009
18	0.009	0.029	0.090	0.166	0.402	1.30	0.120	0.122	0.120	0.017	0.017	0.009
19	0.017	0.029	0.090	0.166	0.953	1.30	0.120	0.122	0.090	0.017	0.017	0.009
20	0.017	0.029	0.090	0.166	1.82	1.30	0.120	0.122	0.090	0.017	0.017	0.009
21	0.017	0.029	0.090	0.166	1.69	1.30	0.120	0.122	0.090	0.017	0.017	0.009
22	0.009	0.029	0.090	0.166	1.56	1.30	0.120	0.122	0.090	0.017	0.017	0.009
23	0.017	0.029	0.090	0.166	1.30	1.30	0.120	0.122	0.090	0.017	0.017	0.009
24	0.017	0.029	0.090	0.166	1.43	1.30	0.120	0.122	0.090	0.017	0.017	0.009
25	0.017	0.060	0.090	0.166	1.56	1.30	0.120	0.122	0.090	0.017	0.017	0.009
26	0.017	0.090	0.090	0.166	1.56	1.30	0.120	0.122	0.090	0.017	0.017	0.009
27	0.017	0.060	0.090	0.166	1.30	1.30	0.120	0.122	0.090	0.017	0.017	0.009
28	0.017	0.060	0.090	0.166	1.30	1.30	0.090	0.122	0.090	0.017	0.017	0.009
29	0.017	0.060	0.122	0.166	-----	1.30	0.090	0.122	0.090	0.017	0.017	0.009
30	0.017	0.060	0.166	0.166	-----	1.30	0.090	0.122	0.090	0.017	0.017	0.009
31	0.017	-----	0.166	0.166	-----	1.17	-----	0.122	-----	0.017	0.017	-----
Maks.	0.017	0.120	0.267	0.267	2.96	2.21	1.25	0.334	0.503	0.120	0.122	0.017
Min.	0.009	0.017	0.017	0.122	0.166	1.17	0.029	0.059	0.060	0.003	0.017	0.009
Ortalama	0.012	0.032	0.098	0.179	0.710	1.33	0.344	0.113	0.106	0.026	0.017	0.010
LT/SN/Km2	0.519	1.36	4.21	7.68	30.5	57.0	14.8	4.85	4.53	1.14	0.729	0.409
AKIM mm.	1.39	3.53	11.3	20.6	73.7	153.	38.3	13.0	11.8	3.04	1.95	1.06
MİL. M3	0.032	0.082	0.263	0.480	1.72	3.56	0.892	0.303	0.274	0.071	0.046	0.025

SU YILI (2006) YILLIK TOPLAM AKIM 7.75 MİLYON M3 332 MM. 10.5 LT/SN/Km2

12. Sakarya Havzasi

D12A228 GÜRLEYK D. DEREKÖY

YERİ : **ESKİŞEHİRDEN BOZÜYÜK E VARILIR.ORADAN PAZARYERİNE.PAZAR YERİNDEN 4 KM SONRA ANA YOLDAN SOLA DÖNÜLÜRDEREKÖYE VARILIR**
29°52'0" Doğu - 39°58'0" Kuzey

YAĞIŞ ALANI : **15.80 km2** **YAKLAŞIK KOT : 819 m**

GÖZLEM SÜRESİ : **01.10.1997 - 30.09.2006**

ORTALAMA AKIMLAR : **Gözlem süresinde 0.159 m3/sn. (11 Yıllık) 2006 Su yılında 0.094 m3/sn.**

ANLIK EN ÇOK VE EN AZ AKIMLAR:

2006 Su yılında anlık ençok akım	:	**3.35**	**m3/sn**	**03.03.2006**
2006 Su yılında anlık enaz akım	:	**0.000**	**m3/sn**	**04.10.2005**
Gözlem süresinde anlık ençok akım	:	**3.35**	**m3/sn**	**03.03.2006**
Gözlem süresinde anlık enaz akım	:	**0.000**	**m3/sn**	**22.07.1999**

Akımlar 01 Ekim 2005 'den 30 Eylül 2006' a kadar m3/sn olarak

Gün	Ekim	Kasım	Aralık	Ocak	Şubat	Mart	Nisan	Mayıs	Haziran	Temmuz	Ağustos	Eylül
01	0.005	KURU	0.082	0.082	0.057	1.44	0.082	0.038	0.024	KURU	KURU	KURU
02	0.005	KURU	0.038	0.082	0.057	2.76	0.057	0.057	0.024	KURU	KURU	KURU
03	0.005	0.038	0.038	0.082	0.057	3.06	0.057	0.038	0.024	0.005	KURU	KURU
04	KURU	0.149	0.038	0.082	0.057	1.22	0.057	0.038	0.024	0.005	KURU	KURU
05	KURU	0.149	0.024	0.082	0.057	0.724	0.057	0.038	0.013	0.005	KURU	KURU
06	KURU	0.199	0.024	0.082	0.057	0.480	0.057	0.038	0.024	0.005	KURU	KURU
07	KURU	0.199	0.013	0.082	0.057	0.331	0.038	0.057	0.024	KURU	KURU	KURU
08	KURU	0.199	0.013	0.082	0.057	0.258	0.038	0.057	0.024	KURU	KURU	KURU
09	KURU	0.199	0.013	0.082	0.057	0.199	0.038	0.057	0.024	KURU	KURU	KURU
10	KURU	0.113	0.013	0.082	0.057	0.149	0.038	0.038	0.038	KURU	KURU	KURU
11	KURU	0.057	0.013	0.082	0.057	0.199	0.038	0.038	0.038	KURU	KURU	KURU
12	KURU	0.057	0.013	0.082	0.057	0.641	0.038	0.038	0.038	KURU	KURU	KURU
13	KURU	0.057	0.013	0.082	0.057	0.557	0.057	0.038	0.038	KURU	KURU	KURU
14	KURU	0.057	0.013	0.082	0.057	0.331	0.082	0.057	0.038	KURU	KURU	KURU
15	KURU	0.057	0.013	0.082	0.057	0.258	0.331	0.038	0.038	KURU	KURU	KURU
16	KURU	0.057	0.013	0.057	0.057	0.199	0.331	0.149	0.038	KURU	KURU	KURU
17	KURU	0.057	0.013	0.057	0.057	0.199	0.480	0.082	0.024	KURU	KURU	KURU
18	KURU	0.057	0.013	0.057	0.057	0.149	0.113	0.057	0.024	KURU	KURU	KURU
19	KURU	0.057	0.024	0.057	0.199	0.113	0.057	0.057	0.013	KURU	KURU	KURU
20	KURU	0.057	0.024	0.057	0.557	0.149	0.057	0.057	0.024	KURU	KURU	KURU
21	KURU	0.057	0.024	0.057	0.805	0.113	0.057	0.038	0.024	KURU	KURU	KURU
22	KURU	0.057	0.024	0.057	0.805	0.113	0.038	0.038	0.024	KURU	KURU	KURU
23	KURU	0.057	0.024	0.057	0.805	0.113	0.038	0.038	0.024	KURU	KURU	KURU
24	KURU	0.082	0.024	0.057	0.805	0.113	0.038	0.038	0.024	KURU	KURU	KURU
25	KURU	0.113	0.024	0.057	1.06	0.113	0.038	0.038	0.024	KURU	KURU	KURU
26	KURU	0.199	0.024	0.057	1.06	0.082	0.038	0.038	0.024	KURU	KURU	KURU
27	KURU	0.113	0.024	0.057	1.06	0.082	0.038	0.038	0.013	KURU	KURU	KURU
28	KURU	0.082	0.057	0.057	0.973	0.082	0.038	0.038	0.024	KURU	KURU	KURU
29	KURU	0.082	0.082	0.057	-----	0.082	0.038	0.038	0.024	KURU	KURU	KURU
30	KURU	0.082	0.082	0.057	-----	0.082	0.038	0.038	KURU	KURU	KURU	KURU
31	KURU	-----	0.082	0.057	-----	0.082	-----	0.024	-----	KURU	KURU	-----
Maks.	0.005	0.480	0.149	0.082	1.83	3.35	0.724	0.258	0.038	0.005	KURU	KURU
Min.	KURU	KURU	KURU	0.057	0.057	0.082	KURU	0.013	KURU	KURU	KURU	KURU
Ortalama	0.000	0.091	0.030	0.069	0.327	0.467	0.083	0.047	0.025	0.001	KURU	KURU
LT/SN/Km2	0.031	5.78	1.88	4.37	20.7	29.5	5.28	3.00	1.61	0.041	0.000	0.000
AKIM mm.	0.082	15.0	5.03	11.7	50.1	79.1	13.7	8.04	4.16	0.109	0.000	0.000
MİL. M3	0.001	0.237	0.079	0.185	0.791	1.25	0.216	0.127	0.066	0.002	0.000	0.000

SU YILI (2006) YILLIK TOPLAM AKIM 2.95 MİLYON M3 187 MM. 5.9 LT/SN/Km2

12. Sakarya Havzasi

D12A230 KARAKAYA D. DOĞANTEPE

YERİ : **ADAPAZARI-DOĞANTEPE ARASINDA 44 KM MESAFEDEDİR**
30°22'10" Doğu - 40°29'30" Kuzey

YAĞIŞ ALANI : **56.00 km2** **YAKLAŞIK KOT : 192 m**

GÖZLEM SÜRESİ : **01.10.1997 - 30.09.2006**

ORTALAMA AKIMLAR : **Gözlem süresinde 0.380 m3/sn. (7 Yıllık) 2006 Su yılında 0.326 m3/sn.**

ANLIK EN ÇOK VE EN AZ AKIMLAR:

2006 Su yılında anlık ençok akım	**:**	**9.60**	**m3/sn**	**11.02.2006**
2006 Su yılında anlık enaz akım	**:**	**0.002**	**m3/sn**	**16.10.2005**
Gözlem süresinde anlık ençok akım	**:**	**9.60**	**m3/sn**	**11.02.2006**
Gözlem süresinde anlık enaz akım	**:**	**0.000**	**m3/sn**	**14.10.2003**

Akımlar 01 Ekim 2005 'den 30 Eylül 2006' a kadar m3/sn olarak

Gün	Ekim	Kasım	Aralık	Ocak	Şubat	Mart	Nisan	Mayıs	Haziran	Temmuz	Ağustos	Eylül
01	0.010	0.023	0.046	0.702	0.602	0.535	0.535	0.392	0.249	0.249	0.107	0.059
02	0.009	0.023	0.046	0.702	0.602	0.535	0.535	0.392	0.249	0.249	0.107	0.059
03	0.007	0.023	0.046	0.502	0.602	1.23	0.535	0.392	0.249	0.249	0.107	0.059
04	0.005	0.023	0.046	0.502	0.602	0.768	0.487	0.392	0.249	0.202	0.107	0.059
05	0.005	0.028	0.046	0.502	0.702	0.535	0.487	0.392	0.249	0.202	0.107	0.059
06	0.005	0.028	0.046	0.502	1.27	0.535	0.487	0.392	0.202	0.202	0.107	0.059
07	0.004	0.037	0.041	0.502	0.901	0.535	0.487	0.392	0.202	0.202	0.107	0.059
08	0.003	0.023	0.041	0.502	0.801	1.00	0.487	0.392	0.202	0.202	0.107	0.059
09	0.003	0.023	0.046	0.502	0.801	1.00	0.487	0.392	0.297	0.202	0.107	0.059
10	0.003	0.023	0.046	0.403	2.63	1.23	0.345	0.392	0.297	0.202	0.107	0.059
11	0.003	0.023	0.046	0.403	6.34	1.00	0.345	0.392	0.297	0.154	0.107	0.059
12	0.003	0.023	0.046	0.303	1.70	1.00	0.345	0.392	0.297	0.154	0.107	0.059
13	0.003	0.023	0.046	0.303	1.23	1.00	0.345	0.392	0.297	0.154	0.107	0.059
14	0.003	0.023	0.046	0.303	1.23	1.00	0.249	0.392	0.297	0.154	0.107	0.059
15	0.002	0.023	0.046	0.303	1.00	1.00	0.249	0.345	0.297	0.154	0.107	0.059
16	0.002	0.023	0.046	0.303	1.00	1.00	0.249	0.345	0.297	0.107	0.107	0.059
17	0.002	0.023	0.089	0.204	1.00	1.00	0.249	0.345	0.249	0.154	0.107	0.059
18	0.003	0.032	0.046	0.204	1.00	0.768	0.249	0.345	0.202	0.154	0.107	0.059
19	0.002	0.023	0.132	0.801	1.47	1.00	0.249	0.345	0.202	0.154	0.059	0.059
20	0.002	0.037	0.110	0.901	1.93	0.768	0.392	0.345	0.202	0.154	0.059	0.059
21	0.002	0.041	0.089	0.702	1.23	0.768	0.392	0.345	0.202	0.154	0.059	0.059
22	0.002	0.032	0.089	0.702	1.00	0.535	0.392	0.297	0.202	0.154	0.059	0.059
23	0.002	0.032	0.089	0.702	1.00	0.535	0.392	0.297	0.202	0.107	0.059	0.059
24	0.002	0.041	0.089	0.702	0.768	0.535	0.392	0.249	0.202	0.107	0.059	0.059
25	0.023	0.046	0.089	0.702	0.768	0.535	0.392	0.249	0.202	0.107	0.059	0.059
26	0.021	0.089	0.132	0.702	0.768	0.535	0.392	0.249	0.202	0.107	0.059	0.051
27	0.021	0.046	0.227	0.702	0.768	0.535	0.392	0.249	0.202	0.107	0.059	0.036
28	0.021	0.037	0.450	0.702	0.535	0.535	0.392	0.249	0.202	0.107	0.059	0.036
29	0.021	0.067	0.706	0.702	-----	0.535	0.392	0.249	0.202	0.107	0.059	0.051
30	0.023	0.067	0.450	0.702	-----	0.535	0.392	0.202	0.202	0.107	0.059	0.044
31	0.023	-----	0.702	0.702	-----	0.535	-----	0.297	-----	0.107	0.059	-----
Maks.	0.227	0.980	2.12	3.40	9.60	4.08	0.535	4.57	0.345	0.249	0.154	0.249
Min.	0.002	0.023	0.041	0.204	0.502	0.487	0.249	0.051	0.202	0.107	0.059	0.029
Ortalama	0.008	0.034	0.136	0.551	1.22	0.760	0.390	0.338	0.237	0.159	0.087	0.056
LT/SN/Km2	0.138	0.598	2.43	9.83	21.8	13.6	6.97	6.04	4.23	2.84	1.55	1.01
AKIM mm.	0.370	1.55	6.50	26.3	52.8	36.3	18.1	16.2	11.0	7.60	4.15	2.61
MİL. M3	0.021	0.087	0.364	1.47	2.96	2.04	1.01	0.906	0.614	0.426	0.233	0.146

SU YILI (2006) YILLIK TOPLAM AKIM 10.28 MİLYON M3 184 MM. 5.8 LT/SN/Km2

12. Sakarya Havzasi

D12A232 KARLANBOĞAZI D. HACCAĞIZ

YERİ : **BOLU-KIBRISCIK YOLUNDA KUZGÖLCÜK KÖYÜNDEN TAKRİBEN 10 KM. SONRA KARAYOLLARI KÖPRÜSÜNÜN MANSABINDADIR.**
31°42'18" Doğu - 40°31'47" Kuzey

YAĞIŞ ALANI : **36.00 km2** **YAKLAŞIK KOT : 1439 m**

GÖZLEM SÜRESİ : **15.12.1998 - 30.09.2006**

ORTALAMA AKIMLAR : **Gözlem süresinde 0.523 m3/sn. (5 Yıllık) 2006 Su yılında 0.407 m3/sn.**

ANLIK EN ÇOK VE EN AZ AKIMLAR:

2006 Su yılında anlık ençok akım	:	**3.25**	**m3/sn**	**12.04.2006**
2006 Su yılında anlık enaz akım	:	**0.000**	**m3/sn**	**19.08.2006**
Gözlem süresinde anlık ençok akım	:	**9.07**	**m3/sn**	**17.04.2002**
Gözlem süresinde anlık enaz akım	:	**0.000**	**m3/sn**	**06.08.2001**

İstasyon için kullanılmış anahtar bulunamadı.

Akımlar 01 Ekim 2005 'den 30 Eylül 2006' a kadar m3/sn olarak

Gün	Ekim	Kasım	Aralık	Ocak	Şubat	Mart	Nisan	Mayıs	Haziran	Temmuz	Ağustos	Eylül
01	0.008	0.045	0.750	0.260	0.320	0.320	1.12	1.37	0.200	0.074	0.074	0.008
02	0.008	0.024	0.560	0.200	0.320	0.560	0.860	1.37	0.150	0.074	0.074	0.008
03	0.024	0.024	0.560	0.470	0.320	0.988	0.650	1.24	0.150	0.150	0.045	0.008
04	0.045	0.024	0.560	0.470	0.320	1.37	0.650	1.12	0.150	0.200	0.045	0.024
05	0.024	0.024	0.470	0.470	0.320	0.750	0.560	0.988	0.108	0.108	0.045	0.024
06	0.024	0.024	0.390	0.560	0.320	0.860	0.750	0.860	0.108	0.074	0.074	0.024
07	0.024	0.024	0.320	0.560	0.320	0.988	0.860	0.860	0.150	0.074	0.045	0.024
08	0.008	0.024	0.260	0.470	0.320	1.24	1.37	0.860	0.150	0.074	0.045	0.008
09	0.008	0.024	0.260	0.390	0.320	1.12	1.84	0.860	0.108	0.074	0.045	0.008
10	0.008	0.024	0.200	0.320	0.320	1.12	1.50	0.750	0.108	0.074	0.045	0.008
11	0.024	0.024	0.150	0.320	0.320	0.988	1.50	0.650	0.150	0.074	0.045	0.008
12	0.024	0.024	0.150	0.320	0.320	0.470	1.84	0.650	0.200	0.074	0.045	0.008
13	0.024	0.024	0.108	0.320	0.320	0.560	2.71	0.750	0.108	0.074	0.045	0.008
14	0.024	0.045	0.074	0.320	0.320	0.650	2.18	0.750	0.108	0.074	0.024	0.008
15	0.024	0.045	0.074	0.320	0.320	0.860	1.67	0.650	0.108	0.074	0.045	0.008
16	0.024	0.045	0.108	0.320	0.320	0.988	1.50	0.650	0.074	0.074	0.045	0.008
17	0.024	0.045	0.074	0.320	0.320	1.12	1.84	0.750	0.074	0.074	0.024	0.008
18	0.024	0.150	0.108	0.320	0.320	1.24	2.01	0.750	0.074	0.074	0.008	0.008
19	0.024	0.320	0.320	0.320	0.320	1.24	2.18	0.650	0.074	0.074	KURU	0.008
20	0.024	1.12	0.320	0.320	0.320	1.24	2.35	0.650	0.074	0.074	KURU	0.024
21	0.024	0.650	0.320	0.320	0.320	1.24	2.71	0.650	0.108	0.074	KURU	0.024
22	0.024	0.470	0.320	0.320	0.320	1.37	2.35	0.650	0.200	0.074	KURU	0.024
23	0.024	0.470	0.320	0.320	0.320	1.37	2.18	0.650	0.150	0.108	KURU	0.024
24	0.024	0.390	0.320	0.320	0.320	1.37	2.01	0.560	0.108	0.108	KURU	0.024
25	0.045	0.560	0.320	0.320	0.320	1.24	1.84	0.470	0.108	0.074	KURU	0.024
26	0.045	1.12	0.320	0.320	0.320	0.988	1.37	0.470	0.108	0.074	KURU	0.024
27	0.045	1.67	0.320	0.320	0.320	0.860	1.12	0.390	0.074	0.074	KURU	0.008
28	0.045	1.67	0.320	0.320	0.320	0.860	0.988	0.320	0.074	0.074	KURU	0.008
29	0.045	1.37	0.320	0.320	-----	0.860	0.988	0.260	0.074	0.074	KURU	0.024
30	0.045	0.988	0.200	0.320	-----	0.988	1.24	0.260	0.074	0.045	KURU	0.008
31	0.045	-----	0.200	0.320	-----	1.37	-----	0.200	-----	0.108	KURU	-----
Maks.	0.074	2.35	0.860	0.560	0.320	2.18	3.25	1.67	0.320	0.560	0.108	0.074
Min.	0.008	0.024	0.045	0.200	0.320	0.320	0.390	0.200	0.024	0.045	KURU	0.008
Ortalama	0.027	0.382	0.293	0.351	0.320	1.01	1.56	0.712	0.117	0.084	0.026	0.014
LT/SN/Km2	0.746	10.6	8.15	9.76	8.89	27.9	43.3	19.8	3.24	2.33	0.733	0.400
AKIM mm.	2.00	27.5	21.8	26.1	21.5	74.9	112.	52.9	8.41	6.25	1.96	1.04
MİL. M3	0.072	0.990	0.786	0.941	0.774	2.69	4.04	1.91	0.303	0.225	0.071	0.037

SU YILI (2006) YILLIK TOPLAM AKIM 12.84 MİLYON M3 357 MM. 11.3 LT/SN/Km2

12. Sakarya Havzasi

D12A235 DEĞİRMENDERE DUDAŞ

YERİ : **ESKISEHIR-SOGUT KARAYOLUNU TAKIBEN OLUKLU KOYUNDEN 5 KMSONRA KOPRUNUN 30 M. MANSABINDADIR**

30°14'0" Doğu - 39°57'0" Kuzey

YAĞIŞ ALANI : **39.63 km2** **YAKLAŞIK KOT : 940 m**

GÖZLEM SÜRESİ : **01.10.1999 - 30.09.2006**

ORTALAMA AKIMLAR : **Gözlem süresinde 0.172 m3/sn. (11 Yıllık) 2006 Su yılında 0.094 m3/sn.**

ANLIK EN ÇOK VE EN AZ AKIMLAR:

2006 Su yılında anlık ençok akım	**:**	**1.44**	**m3/sn**	**03.03.2006**
2006 Su yılında anlık enaz akım	**:**	**0.000**	**m3/sn**	**09.09.2006**
Gözlem süresinde anlık ençok akım	**:**	**3.48**	**m3/sn**	**27.02.2004**
Gözlem süresinde anlık enaz akım	**:**	**0.000**	**m3/sn**	**01.10.2001**

Akımlar 01 Ekim 2005 'den 30 Eylül 2006' a kadar m3/sn olarak

Gün	Ekim	Kasım	Aralık	Ocak	Şubat	Mart	Nisan	Mayıs	Haziran	Temmuz	Ağustos	Eylül
01	0.014	0.014	0.022	0.033	0.022	0.442	0.267	0.237	0.116	0.033	0.014	0.008
02	0.014	0.014	0.022	0.022	0.022	0.403	0.267	0.237	0.116	0.033	0.014	0.008
03	0.014	0.014	0.022	0.022	0.022	0.688	0.267	0.237	0.116	0.033	0.014	0.008
04	0.014	0.014	0.022	0.022	0.033	0.481	0.267	0.237	0.095	0.033	0.014	0.008
05	0.014	0.014	0.033	0.022	0.033	0.403	0.267	0.237	0.074	0.022	0.014	0.008
06	0.014	0.014	0.045	0.022	0.033	0.325	0.267	0.237	0.074	0.022	0.014	0.008
07	0.014	0.014	0.022	0.022	0.033	0.325	0.237	0.237	0.074	0.033	0.014	0.008
08	0.014	0.014	0.022	0.022	0.033	0.364	0.237	0.237	0.074	0.033	0.014	0.001
09	0.014	0.014	0.022	0.022	0.033	0.325	0.237	0.237	0.074	0.033	0.014	KURU
10	0.014	0.014	0.022	0.022	0.033	0.296	0.237	0.208	0.074	0.033	0.014	KURU
11	0.014	0.014	0.022	0.022	0.033	0.325	0.237	0.208	0.059	0.022	0.014	KURU
12	0.014	0.022	0.022	0.022	0.045	0.632	0.237	0.208	0.059	0.022	0.014	KURU
13	0.014	0.022	0.022	0.022	0.045	0.632	0.237	0.208	0.059	0.022	0.014	KURU
14	0.014	0.022	0.022	0.022	0.045	0.520	0.237	0.208	0.074	0.022	0.014	KURU
15	0.014	0.022	0.033	0.022	0.045	0.520	0.237	0.208	0.074	0.022	0.014	KURU
16	0.014	0.022	0.022	0.022	0.045	0.442	0.237	0.208	0.074	0.022	0.014	KURU
17	0.014	0.022	0.033	0.022	0.059	0.442	0.237	0.208	0.074	0.022	0.014	KURU
18	0.014	0.022	0.022	0.022	0.059	0.403	0.237	0.208	0.074	0.022	0.014	KURU
19	0.014	0.022	0.022	0.022	0.059	0.403	0.237	0.179	0.074	0.022	0.014	KURU
20	0.014	0.022	0.022	0.022	0.074	0.403	0.237	0.179	0.074	0.022	0.014	KURU
21	0.014	0.022	0.014	0.022	0.137	0.364	0.237	0.179	0.074	0.014	0.014	KURU
22	0.014	0.022	0.022	0.022	0.179	0.325	0.237	0.179	0.059	0.014	0.014	KURU
23	0.014	0.022	0.022	0.022	0.208	0.296	0.237	0.158	0.059	0.014	0.014	KURU
24	0.014	0.022	0.022	0.022	0.237	0.296	0.237	0.137	0.045	0.014	0.014	KURU
25	0.014	0.022	0.022	0.022	0.364	0.325	0.237	0.137	0.033	0.014	0.014	KURU
26	0.014	0.022	0.022	0.022	0.520	0.296	0.237	0.137	0.033	0.014	0.014	KURU
27	0.014	0.022	0.022	0.022	0.442	0.267	0.237	0.137	0.033	0.014	0.014	KURU
28	0.014	0.022	0.022	0.022	0.403	0.267	0.237	0.137	0.033	0.014	0.014	KURU
29	0.014	0.022	0.033	0.022	-----	0.267	0.237	0.137	0.033	0.014	0.014	KURU
30	0.014	0.022	0.033	0.022	-----	0.267	0.237	0.116	0.033	0.014	0.014	KURU
31	0.014	-----	0.033	0.022	-----	0.267	-----	0.116	-----	0.014	0.008	-----
Maks.	0.014	0.022	0.208	0.033	0.688	1.44	0.325	0.237	0.116	0.033	0.014	0.008
Min.	0.014	0.014	0.014	0.022	0.022	0.267	0.208	0.116	0.033	0.014	0.008	KURU
Ortalama	0.014	0.019	0.025	0.022	0.118	0.387	0.243	0.191	0.067	0.022	0.014	0.002
LT/SN/Km2	0.353	0.481	0.621	0.564	2.97	9.78	6.13	4.83	1.70	0.555	0.348	0.048
AKIM mm.	0.946	1.25	1.66	1.51	7.19	26.2	15.9	12.9	4.40	1.49	0.933	0.124
MİL. M3	0.037	0.049	0.066	0.060	0.285	1.04	0.630	0.513	0.174	0.059	0.037	0.005

SU YILI (2006) YILLIK TOPLAM AKIM 2.95 MİLYON M3 75 MM. 2.4 LT/SN/Km2

12. Sakarya Havzasi

D12A238 ANKARA ÇAYI ESENKENT

YERİ : **ANKARA AYAŞ YOLUNUN YENİKENT GİRİŞİNDEN SOLA DÖNÜLEN YOLUN 17.KM SİNDEKİ ASKİ ARITMA TESİSLERİNİN İÇİNDEDİR.**
32°27'52" Doğu - 39°53'22" Kuzey

YAĞIŞ ALANI : **4990.10 km2** **YAKLAŞIK KOT : 755 m**

GÖZLEM SÜRESİ : **25.12.2000 - 30.09.2006**

ORTALAMA AKIMLAR : **Gözlem süresinde 12.681 m3/sn. (4 Yıllık) 2006 Su yılında 13.681 m3/sn.**

ANLIK EN ÇOK VE EN AZ AKIMLAR:

2006 Su yılında anlık ençok akım	**:**	**36.3**	**m3/sn**	**10.02.2006**
2006 Su yılında anlık enaz akım	**:**	**5.70**	**m3/sn**	**14.07.2006**
Gözlem süresinde anlık ençok akım	**:**	**59.2**	**m3/sn**	**09.02.2003**
Gözlem süresinde anlık enaz akım	**:**	**5.70**	**m3/sn**	**03.07.2004**

İstasyon için kullanılmış anahtar bulunamadı.

Akımlar 01 Ekim 2005 'den 30 Eylül 2006' a kadar m3/sn olarak

Gün	Ekim	Kasım	Aralık	Ocak	Şubat	Mart	Nisan	Mayıs	Haziran	Temmuz	Ağustos	Eylül
01	11.3	12.9	11.3	14.0	13.5	19.4	21.4	18.2	11.3	9.86	9.86	9.38
02	11.8	14.6	11.3	13.5	13.5	19.4	21.4	19.4	11.3	9.86	9.38	11.3
03	12.4	14.6	11.8	13.5	13.5	22.1	21.4	19.4	11.3	10.3	9.38	9.86
04	23.5	13.5	11.8	13.5	12.9	24.3	20.7	17.0	10.8	11.3	9.38	8.49
05	14.6	17.0	11.3	14.6	13.5	22.1	19.4	16.4	11.3	10.3	9.38	8.90
06	13.5	17.0	10.8	14.6	15.2	22.1	19.4	17.0	12.4	10.3	9.38	8.90
07	12.9	14.6	11.3	14.0	19.4	20.0	18.2	17.6	10.3	10.3	8.90	8.49
08	12.4	14.0	11.3	14.0	17.6	20.7	18.2	17.0	9.38	10.3	8.49	8.90
09	12.9	13.5	11.3	13.5	18.8	27.5	18.2	17.6	11.8	9.38	9.38	8.90
10	12.9	12.9	11.3	13.5	17.0	24.3	18.2	17.6	14.6	9.86	9.38	8.90
11	12.9	12.9	11.3	12.4	22.8	22.8	17.6	17.6	12.4	10.3	9.38	8.90
12	12.9	11.3	11.3	11.8	27.5	22.8	18.2	17.0	9.86	10.8	9.86	8.90
13	13.5	12.4	10.8	11.8	20.0	22.8	18.2	17.0	10.3	9.86	8.49	8.90
14	13.5	14.0	10.8	12.4	17.6	21.4	19.4	15.8	12.4	9.38	8.90	9.38
15	12.9	14.0	10.8	12.4	16.4	20.7	21.4	14.6	11.3	9.38	8.49	9.38
16	12.9	14.6	11.3	13.5	15.8	20.7	18.8	13.5	9.86	8.90	8.49	9.38
17	12.9	13.5	12.9	13.5	15.2	21.4	18.2	14.0	10.3	8.90	8.49	9.38
18	12.9	15.2	11.3	13.5	15.8	20.0	17.6	14.0	10.3	8.90	8.90	9.86
19	12.9	13.5	11.8	14.6	17.6	25.9	17.0	12.4	10.3	9.38	8.90	9.38
20	15.8	17.0	12.9	16.4	20.0	22.8	17.0	10.8	10.3	9.38	8.90	9.86
21	14.0	18.2	12.4	14.0	20.0	20.0	16.4	11.3	10.3	9.38	8.08	11.8
22	14.0	15.8	11.8	13.5	18.8	20.0	15.8	11.3	10.8	8.90	8.08	10.8
23	13.5	14.0	11.8	14.0	17.6	20.0	17.6	11.3	9.86	8.49	8.49	10.8
24	13.5	12.9	12.4	13.5	17.0	21.4	17.6	11.3	10.3	8.49	8.49	10.8
25	15.8	11.3	12.4	13.5	17.0	20.7	17.0	10.8	10.8	8.49	8.49	18.2
26	13.5	11.3	12.4	13.5	17.6	21.4	17.0	10.8	10.3	8.08	8.90	10.8
27	13.5	11.3	12.9	13.5	22.8	22.8	17.0	11.3	10.8	8.08	9.86	9.38
28	12.4	11.8	12.9	13.5	20.0	22.1	17.0	11.3	10.8	8.08	8.90	9.86
29	12.4	11.3	13.5	13.5	-----	20.7	18.2	10.3	10.8	8.08	8.49	11.3
30	12.4	11.3	12.9	13.5	-----	20.7	19.4	10.8	10.8	8.90	8.90	22.1
31	12.9	-----	13.5	13.5	-----	21.4	-----	11.3	-----	9.38	8.49	-----
Maks.	23.5	18.2	18.2	22.1	36.3	33.4	27.5	24.3	21.4	15.8	13.5	34.4
Min.	11.3	11.3	9.86	9.86	11.8	17.0	13.5	6.45	6.85	5.70	5.70	6.85
Ortalama	13.5	13.7	11.9	13.6	17.7	21.8	18.4	14.4	10.9	9.40	8.93	10.4
LT/SN/Km2	2.71	2.75	2.38	2.72	3.54	4.36	3.69	2.88	2.19	1.88	1.79	2.08
AKIM mm.	7.26	7.14	6.36	7.28	8.56	11.7	9.57	7.72	5.67	5.04	4.79	5.39
MİL. M3	36.2	35.6	31.8	36.3	42.7	58.3	47.8	38.5	28.3	25.2	23.9	26.9

SU YILI (2006) YILLIK TOPLAM AKIM 431.50 MİLYON M3 86 MM. 2.7 LT/SN/Km2

12. Sakarya Havzasi

D12A240 İLHAN ÇAYI BAYAT

YERİ : **ANKARA-AYAŞ YOLUNDAN ÇANILLI BELDESİNE DÖNÜLÜR.İSTASYON ÇANILLI GÖLETİNİN MENBASINDA İLHAN ÇAYI ÜZERİNDE BAYAT KÖYÜ GİRİŞİNDEKİ KÖPRÜNÜN 50 M. MENBASINDADIR. 32°26'29" Doğu - 40°10'58" Kuzey**

YAĞIŞ ALANI : **108.56 km2** **YAKLAŞIK KOT : 1020 m**

GÖZLEM SÜRESİ : **27.11.2002 - 30.09.2006**

ORTALAMA AKIMLAR : **Gözlem süresinde 0.238 m3/sn. (3 Yıllık) 2006 Su yılında 0.196 m3/sn.**

ANLIK EN ÇOK VE EN AZ AKIMLAR:

2006 Su yılında anlık ençok akım	**:**	**11.5**	**m3/sn**	**03.03.2006**
2006 Su yılında anlık enaz akım	**:**	**0.003**	**m3/sn**	**20.07.2006**
Gözlem süresinde anlık ençok akım	**:**	**11.5**	**m3/sn**	**03.03.2006**
Gözlem süresinde anlık enaz akım	**:**	**0.002**	**m3/sn**	**23.07.2004**

İstasyon için kullanılmış anahtar bulunamadı.

Akımlar 01 Ekim 2005 'den 30 Eylül 2006' a kadar m3/sn olarak

Gün	Ekim	Kasım	Aralık	Ocak	Şubat	Mart	Nisan	Mayıs	Haziran	Temmuz	Ağustos	Eylül
01	0.010	0.060	0.060	0.085	0.085	3.12	0.360	0.270	0.110	0.010	0.007	0.007
02	0.010	0.060	0.060	0.085	0.085	2.44	0.315	0.270	0.110	0.010	0.007	0.007
03	0.035	0.060	0.060	0.085	0.085	6.70	0.315	0.270	0.110	0.010	0.007	0.007
04	0.035	0.060	0.060	0.085	0.085	2.29	0.315	0.225	0.110	0.010	0.007	0.007
05	0.035	0.060	0.060	0.085	0.085	1.36	0.315	0.225	0.110	0.010	0.007	0.007
06	0.035	0.060	0.060	0.110	0.085	1.20	0.315	0.225	0.110	0.010	0.007	0.007
07	0.035	0.060	0.060	0.135	0.110	1.10	0.270	0.225	0.110	0.010	0.007	0.007
08	0.035	0.060	0.060	0.110	0.110	1.20	0.270	0.225	0.085	0.010	0.007	0.007
09	0.035	0.060	0.085	0.110	0.110	1.01	0.270	0.225	0.085	0.010	0.007	0.007
10	0.035	0.060	0.085	0.110	0.110	0.576	0.270	0.225	0.085	0.010	0.007	0.007
11	0.035	0.060	0.085	0.085	0.315	0.504	0.270	0.225	0.085	0.010	0.007	0.007
12	0.035	0.060	0.085	0.085	0.360	0.576	0.270	0.225	0.085	0.007	0.007	0.007
13	0.035	0.060	0.085	0.085	0.315	0.576	0.270	0.225	0.060	0.007	0.007	0.007
14	0.035	0.060	0.085	0.085	0.270	0.576	0.270	0.225	0.060	0.007	0.007	0.007
15	0.035	0.060	0.085	0.085	0.270	0.504	0.270	0.225	0.060	0.007	0.007	0.007
16	0.035	0.060	0.085	0.085	0.270	0.432	0.270	0.225	0.060	0.007	0.007	0.007
17	0.035	0.060	0.085	0.085	0.270	0.576	0.270	0.225	0.035	0.007	0.007	0.007
18	0.035	0.060	0.085	0.085	0.180	0.720	0.270	0.225	0.035	0.007	0.007	0.007
19	0.060	0.060	0.085	0.085	0.180	0.648	0.270	0.225	0.035	0.007	0.007	0.007
20	0.060	0.060	0.085	0.110	0.225	0.504	0.270	0.180	0.035	0.007	0.007	0.007
21	0.060	0.060	0.085	0.110	0.360	0.432	0.225	0.180	0.010	0.007	0.007	0.007
22	0.060	0.060	0.085	0.110	0.576	0.432	0.225	0.180	0.010	0.007	0.007	0.007
23	0.060	0.060	0.085	0.110	0.648	0.504	0.225	0.180	0.010	0.007	0.007	0.007
24	0.060	0.060	0.085	0.110	0.720	0.816	0.270	0.180	0.010	0.007	0.007	0.007
25	0.060	0.060	0.060	0.085	1.01	0.648	0.225	0.180	0.010	0.007	0.007	0.007
26	0.060	0.060	0.085	0.085	2.94	0.576	0.225	0.180	0.010	0.007	0.007	0.007
27	0.060	0.060	0.085	0.085	2.94	0.504	0.225	0.135	0.010	0.007	0.003	0.007
28	0.060	0.060	0.085	0.085	1.51	0.432	0.225	0.135	0.010	0.007	0.007	0.007
29	0.060	0.060	0.085	0.085	-----	0.432	0.225	0.135	0.010	0.007	0.007	0.007
30	0.060	0.060	0.085	0.085	-----	0.360	0.270	0.135	0.010	0.007	0.003	0.010
31	0.060	-----	0.085	0.085	-----	0.360	-----	0.135	-----	0.007	0.007	-----
Maks.	0.060	0.085	0.085	0.225	6.31	11.5	0.360	0.270	0.110	0.035	0.007	0.010
Min.	0.010	0.060	0.060	0.085	0.085	0.360	0.225	0.135	0.010	0.003	0.003	0.007
Ortalama	0.044	0.060	0.078	0.094	0.511	1.04	0.268	0.205	0.056	0.008	0.007	0.007
LT/SN/Km2	0.404	0.553	0.716	0.865	4.71	9.54	2.47	1.89	0.514	0.074	0.062	0.065
AKIM mm.	1.08	1.43	1.92	2.32	11.4	25.6	6.41	5.05	1.33	0.199	0.166	0.170
MİL. M3	0.118	0.156	0.208	0.251	1.24	2.77	0.696	0.548	0.145	0.022	0.018	0.018

SU YILI (2006) YILLIK TOPLAM AKIM 6.19 MİLYON M3 57 MM. 1.8 LT/SN/Km2

12. Sakarya Havzasi

D12A242 MERA ÇAYI UĞURLU

YERİ : **ANKARA-KIZILCAHAMAM YOLUNUN 62. KM SİNDE YOLUN SAĞINDA MERA ÇAYI ÜZERİNDEDİR. 32°40'54" Doğu - 40°21'2" Kuzey**

YAĞIŞ ALANI : **120.90 km2** **YAKLAŞIK KOT : 1015 m**

GÖZLEM SÜRESİ : **01.10.2003 - 30.09.2006**

ORTALAMA AKIMLAR : **Gözlem süresinde 0.492 m3/sn. (3 Yıllık) 2006 Su yılında 0.392 m3/sn.**

ANLIK EN ÇOK VE EN AZ AKIMLAR:

2006 Su yılında anlık ençok akım	**:**	**19.7**	**m3/sn**	**03.03.2006**
2006 Su yılında anlık enaz akım	**:**	**0.009**	**m3/sn**	**18.09.2006**
Gözlem süresinde anlık ençok akım	**:**	**21.4**	**m3/sn**	**03.03.2005**
Gözlem süresinde anlık enaz akım	**:**	**0.009**	**m3/sn**	**18.09.2006**

İstasyon için kullanılmış anahtar bulunamadı.

Akımlar 01 Ekim 2005 'den 30 Eylül 2006' a kadar m3/sn olarak

Gün	Ekim	Kasım	Aralık	Ocak	Şubat	Mart	Nisan	Mayıs	Haziran	Temmuz	Ağustos	Eylül
01	0.045	0.065	0.225	0.225	0.150	5.80	1.08	0.150	0.034	0.034	0.034	0.034
02	0.045	0.065	0.225	0.225	0.150	6.08	0.990	0.150	0.034	0.034	0.034	0.034
03	0.065	0.065	0.225	0.225	0.065	10.8	0.900	0.150	0.034	0.065	0.034	0.034
04	0.045	0.065	0.225	0.225	0.065	4.51	0.800	0.225	0.034	0.065	0.034	0.034
05	0.045	0.065	0.225	0.225	0.150	3.08	0.800	0.225	0.034	0.065	0.034	0.034
06	0.045	0.065	0.150	0.385	0.150	3.27	0.700	0.225	0.034	0.065	0.034	0.034
07	0.045	0.065	0.065	0.545	0.225	2.89	0.620	0.150	0.034	0.065	0.034	0.034
08	0.045	0.065	0.065	0.385	0.225	3.46	0.620	0.150	0.034	0.065	0.034	0.034
09	0.045	0.065	0.065	0.305	0.225	3.46	0.620	0.150	0.034	0.065	0.026	0.034
10	0.045	0.065	0.065	0.225	0.225	1.95	0.545	0.150	0.045	0.045	0.020	0.034
11	0.045	0.065	0.065	0.225	0.385	1.59	0.545	0.150	0.065	0.045	0.020	0.045
12	0.045	0.065	0.065	0.225	0.465	1.59	0.465	0.150	0.065	0.034	0.026	0.045
13	0.045	0.065	0.065	0.225	0.305	2.25	0.465	0.150	0.065	0.034	0.034	0.045
14	0.045	0.065	0.065	0.225	0.305	2.40	0.385	0.225	0.065	0.034	0.034	0.034
15	0.045	0.065	0.065	0.150	0.225	2.25	0.465	0.150	0.065	0.034	0.034	0.034
16	0.065	0.065	0.150	0.150	0.225	1.71	0.385	0.150	0.045	0.034	0.026	0.034
17	0.065	0.065	0.225	0.150	0.225	1.59	0.385	0.150	0.045	0.034	0.034	0.034
18	0.065	0.065	0.225	0.150	0.225	1.35	0.305	0.150	0.045	0.034	0.034	0.034
19	0.065	0.065	0.225	0.065	0.225	1.26	0.305	0.150	0.045	0.034	0.034	0.026
20	0.065	0.225	0.225	0.150	0.465	1.08	0.225	0.150	0.034	0.034	0.034	0.026
21	0.065	0.225	0.150	0.150	0.900	0.990	0.225	0.150	0.045	0.034	0.034	0.026
22	0.065	0.150	0.150	0.150	1.26	1.26	0.225	0.150	0.045	0.034	0.034	0.034
23	0.065	0.150	0.150	0.150	1.17	2.10	0.225	0.150	0.045	0.034	0.034	0.045
24	0.065	0.225	0.150	0.150	1.83	2.70	0.305	0.065	0.045	0.034	0.034	0.045
25	0.065	0.225	0.150	0.150	2.10	2.10	0.305	0.065	0.045	0.034	0.034	0.045
26	0.065	0.225	0.150	0.150	4.08	1.71	0.225	0.065	0.034	0.034	0.034	0.045
27	0.065	0.225	0.150	0.150	4.94	1.35	0.225	0.065	0.034	0.034	0.034	0.045
28	0.065	0.225	0.150	0.150	3.27	1.35	0.225	0.065	0.034	0.034	0.034	0.045
29	0.065	0.225	0.150	0.150	-----	1.17	0.225	0.045	0.034	0.034	0.034	0.034
30	0.065	0.225	0.150	0.150	-----	1.17	0.305	0.045	0.034	0.034	0.034	0.045
31	0.065	-----	0.225	0.150	-----	1.26	-----	0.045	-----	0.034	0.034	-----
Maks.	0.065	0.465	0.225	0.700	8.04	19.7	1.35	0.385	0.150	0.065	0.034	0.065
Min.	0.045	0.065	0.065	0.065	0.045	0.990	0.225	0.034	0.034	0.034	0.016	0.009
Ortalama	0.056	0.119	0.150	0.204	0.865	2.57	0.470	0.136	0.043	0.042	0.032	0.037
LT/SN/Km2	0.463	0.982	1.24	1.69	7.16	21.2	3.89	1.12	0.354	0.345	0.267	0.305
AKIM mm.	1.24	2.54	3.31	4.53	17.3	56.8	10.1	3.01	0.918	0.924	0.716	0.790
MİL. M3	0.150	0.308	0.400	0.547	2.09	6.87	1.22	0.364	0.111	0.112	0.087	0.096

SU YILI (2006) YILLIK TOPLAM AKIM 12.36 MİLYON M3 102 MM. 3.2 LT/SN/Km2

12. Sakarya Havzasi

D12A243 KARA DERE ENDİL BOĞAZI

YERİ : **ANKARA-AYAŞ YOLU 34. KM SİNDEN SAĞA, ORTABEREKET KÖYÜNE DÖNDÜKTEN SONRA 5 KM. İLERİSİNDE ASARTEPE BARAJI MENBASINDADIR.**
32°24'46" Doğu - 40°8'53" Kuzey

YAĞIŞ ALANI : **88.10 km2** **YAKLAŞIK KOT : 910 m**

GÖZLEM SÜRESİ : **01.12.2003 - 30.09.2006**

ORTALAMA AKIMLAR : **Gözlem süresinde 0.155 m3/sn. (2 Yıllık) 2006 Su yılında 0.147 m3/sn.**

ANLIK EN ÇOK VE EN AZ AKIMLAR:

2006 Su yılında anlık ençok akım	**:**	**2.25 m3/sn**	**03.03.2006**
2006 Su yılında anlık enaz akım	**:**	**0.013 m3/sn**	**10.08.2006**
Gözlem süresinde anlık ençok akım	**:**	**4.88 m3/sn**	**01.08.2005**
Gözlem süresinde anlık enaz akım	**:**	**0.013 m3/sn**	**19.12.2004**

İstasyon için kullanılmış anahtar bulunamadı.

Akımlar 01 Ekim 2005 'den 30 Eylül 2006' a kadar m3/sn olarak

Gün	Ekim	Kasım	Aralık	Ocak	Şubat	Mart	Nisan	Mayıs	Haziran	Temmuz	Ağustos	Eylül
01	0.124	0.124	0.124	0.124	0.124	0.628	0.221	0.187	0.066	0.093	0.036	0.066
02	0.124	0.124	0.124	0.124	0.066	0.518	0.187	0.187	0.066	0.093	0.036	0.093
03	0.124	0.124	0.124	0.124	0.124	1.40	0.187	0.187	0.066	0.154	0.036	0.093
04	0.124	0.124	0.124	0.124	0.124	0.738	0.154	0.187	0.066	0.093	0.036	0.093
05	0.124	0.124	0.124	0.124	0.124	0.518	0.154	0.187	0.093	0.066	0.036	0.093
06	0.124	0.124	0.124	0.124	0.124	0.473	0.154	0.187	0.093	0.066	0.036	0.093
07	0.124	0.124	0.124	0.124	0.124	0.427	0.154	0.187	0.093	0.066	0.036	0.093
08	0.124	0.124	0.124	0.124	0.124	0.427	0.154	0.187	0.093	0.066	0.036	0.093
09	0.124	0.124	0.124	0.124	0.124	0.378	0.154	0.187	0.124	0.066	0.036	0.093
10	0.124	0.124	0.124	0.124	0.124	0.336	0.154	0.187	0.093	0.066	0.036	0.066
11	0.124	0.124	0.124	0.124	0.154	0.297	0.154	0.187	0.093	0.066	0.036	0.066
12	0.124	0.124	0.124	0.124	0.154	0.297	0.154	0.187	0.093	0.066	0.036	0.066
13	0.124	0.124	0.124	0.124	0.124	0.297	0.154	0.187	0.093	0.066	0.036	0.093
14	0.154	0.124	0.124	0.124	0.124	0.297	0.154	0.221	0.124	0.066	0.036	0.093
15	0.154	0.124	0.124	0.124	0.124	0.260	0.187	0.221	0.124	0.066	0.036	0.093
16	0.154	0.124	0.124	0.124	0.124	0.260	0.187	0.187	0.124	0.066	0.036	0.093
17	0.154	0.124	0.124	0.124	0.124	0.297	0.187	0.187	0.154	0.066	0.036	0.093
18	0.154	0.124	0.124	0.124	0.124	0.378	0.187	0.187	0.154	0.066	0.036	0.093
19	0.154	0.124	0.124	0.124	0.124	0.427	0.187	0.187	0.124	0.066	0.036	0.093
20	0.154	0.124	0.124	0.124	0.124	0.336	0.187	0.187	0.154	0.066	0.036	0.093
21	0.154	0.124	0.124	0.124	0.154	0.336	0.187	0.154	0.154	0.066	0.036	0.093
22	0.154	0.124	0.124	0.124	0.221	0.297	0.187	0.154	0.154	0.066	0.036	0.093
23	0.124	0.124	0.124	0.124	0.260	0.297	0.187	0.154	0.187	0.066	0.066	0.124
24	0.124	0.124	0.124	0.124	0.260	0.297	0.187	0.154	0.221	0.066	0.066	0.124
25	0.124	0.124	0.124	0.124	0.336	0.297	0.187	0.154	0.187	0.066	0.066	0.124
26	0.124	0.124	0.124	0.124	0.683	0.260	0.187	0.154	0.221	0.066	0.066	0.124
27	0.124	0.124	0.124	0.124	0.793	0.221	0.187	0.154	0.154	0.066	0.066	0.124
28	0.124	0.124	0.124	0.124	0.518	0.221	0.187	0.124	0.066	0.066	0.066	0.124
29	0.124	0.124	0.124	0.124	-----	0.187	0.187	0.124	0.093	0.066	0.066	0.124
30	0.124	0.124	0.124	0.124	-----	0.187	0.187	0.124	0.093	0.066	0.066	0.124
31	0.124	-----	0.124	0.124	-----	0.187	-----	0.093	-----	0.066	0.066	-----
Maks.	0.154	0.187	0.154	0.154	1.25	2.25	0.221	0.221	0.260	1.11	0.066	0.124
Min.	0.124	0.124	0.124	0.093	0.036	0.187	0.154	0.036	0.036	0.066	0.013	0.036
Ortalama	0.133	0.124	0.124	0.124	0.204	0.380	0.176	0.173	0.121	0.071	0.045	0.098
LT/SN/Km2	1.51	1.41	1.41	1.41	2.31	4.31	2.00	1.96	1.37	0.811	0.507	1.11
AKIM mm.	4.03	3.65	3.77	3.77	5.60	11.5	5.18	5.25	3.55	2.17	1.36	2.87
MİL. M3	0.355	0.321	0.332	0.332	0.493	1.02	0.456	0.462	0.313	0.191	0.120	0.253

SU YILI (2006) YILLIK TOPLAM AKIM 4.65 MİLYON M3 53 MM. 1.7 LT/SN/Km2

12. Sakarya Havzasi

D12A244 KİRMİR ÇAYI YEŞİLÖZ KÖPRÜSÜ

YERİ : **YEŞİLÖZ-GÜDÜL KARAYOLU KAMANLAR KÖYÜNE 1,5 KM. MESAFEDEKİ KÖPRÜDEDİR.**
32°15'42" Doğu - 40°14'14" Kuzey

YAĞIŞ ALANI : **2239.00 km2** **YAKLAŞIK KOT : 680 m**

GÖZLEM SÜRESİ : **01.10.2004 - 30.09.2006**

ORTALAMA AKIMLAR : **Gözlem süresinde 3.490 m3/sn. (2 Yıllık) 2006 Su yılında 2.719 m3/sn.**

ANLIK EN ÇOK VE EN AZ AKIMLAR:

2006 Su yılında anlık ençok akım	**:**	**48.7**	**m3/sn**	**05.03.2006**
2006 Su yılında anlık enaz akım	**:**	**0.337**	**m3/sn**	**03.08.2006**
Gözlem süresinde anlık ençok akım	**:**	**48.7**	**m3/sn**	**05.03.2006**
Gözlem süresinde anlık enaz akım	**:**	**0.337**	**m3/sn**	**03.08.2006**

İstasyon için kullanılmış anahtar bulunamadı.

Akımlar 01 Ekim 2005 'den 30 Eylül 2006' a kadar m3/sn olarak

Gün	Ekim	Kasım	Aralık	Ocak	Şubat	Mart	Nisan	Mayıs	Haziran	Temmuz	Ağustos	Eylül
01	1.47	1.09	0.954	0.887	0.887	24.9	7.01	0.887	0.528	0.668	0.369	0.443
02	1.47	1.09	0.954	0.887	0.954	26.5	7.49	0.954	0.528	0.668	0.369	0.443
03	1.47	1.09	0.954	0.954	0.954	29.5	6.58	0.887	0.528	0.668	0.337	0.443
04	1.47	1.09	0.954	0.954	1.15	48.1	5.30	1.02	0.528	0.668	0.337	0.443
05	1.47	1.09	0.954	1.22	1.22	48.7	4.92	1.02	0.528	0.668	0.337	0.443
06	1.47	1.09	0.887	1.55	1.22	26.0	4.23	1.02	0.571	0.723	0.337	0.443
07	1.47	1.09	0.887	1.55	1.38	21.3	3.54	1.22	0.571	0.723	0.337	0.443
08	1.38	1.09	0.887	1.73	1.47	20.4	3.37	1.15	0.571	0.668	0.337	0.443
09	1.38	1.09	0.887	1.63	1.47	20.8	3.24	1.15	0.668	0.668	0.337	0.443
10	1.38	1.15	0.887	1.55	1.38	19.9	3.24	1.15	0.668	0.668	0.337	0.443
11	1.22	1.15	0.887	1.55	1.73	16.8	3.11	1.22	0.668	0.668	0.337	0.443
12	1.22	1.15	0.887	1.55	3.37	13.4	2.84	1.22	0.668	0.668	0.337	0.528
13	1.22	1.15	0.887	1.47	6.16	9.95	2.84	1.22	0.668	0.668	0.369	0.528
14	1.22	1.15	0.887	1.47	4.06	12.0	2.71	1.38	0.668	0.668	0.369	0.528
15	1.15	1.15	0.887	1.38	2.84	13.1	2.71	1.22	0.668	0.668	0.369	0.528
16	1.15	1.15	0.887	1.22	2.59	16.8	2.47	1.30	0.668	0.668	0.369	0.528
17	1.15	1.15	0.887	1.09	2.12	13.4	2.47	1.30	0.668	0.668	0.369	0.528
18	1.15	1.15	0.887	1.09	2.12	12.7	2.36	1.30	0.668	0.571	0.369	0.528
19	1.15	1.15	0.887	1.09	2.24	12.0	2.24	1.09	0.668	0.571	0.369	0.528
20	1.09	1.15	0.887	1.38	1.92	9.40	2.12	1.09	0.668	0.571	0.401	0.528
21	1.09	1.09	0.887	1.22	2.71	7.22	1.73	1.09	0.668	0.528	0.401	0.528
22	1.09	1.09	0.887	1.15	4.92	5.94	1.55	0.954	0.668	0.528	0.401	0.528
23	1.09	1.09	0.887	1.09	7.77	7.22	1.47	0.954	0.668	0.528	0.401	0.528
24	1.09	1.09	0.887	1.22	9.95	10.3	1.47	0.832	0.668	0.443	0.443	0.528
25	1.09	1.09	0.887	1.22	12.7	11.7	1.30	0.832	0.668	0.443	0.443	0.528
26	1.09	1.09	0.887	1.22	13.4	14.7	1.30	0.777	0.668	0.443	0.443	0.528
27	1.09	1.02	0.887	1.09	22.2	13.4	1.15	0.668	0.668	0.443	0.443	0.528
28	1.09	1.02	0.887	1.09	34.0	11.7	1.15	0.668	0.668	0.401	0.443	0.528
29	1.09	1.02	0.887	0.954	-----	9.40	1.02	0.613	0.668	0.401	0.443	0.528
30	1.09	1.02	0.887	0.954	-----	8.59	0.954	0.571	0.668	0.369	0.443	0.528
31	1.09	-----	0.887	0.887	-----	7.49	-----	0.528	-----	0.369	0.443	-----
Maks.	1.47	1.15	0.954	1.73	34.0	48.7	7.49	1.38	0.668	0.723	0.443	0.528
Min.	1.09	1.02	0.887	0.887	0.887	5.94	0.954	0.528	0.528	0.369	0.337	0.443
Ortalama	1.23	1.10	0.898	1.24	5.32	16.9	2.93	1.01	0.635	0.583	0.382	0.497
LT/SN/Km2	0.549	0.492	0.401	0.552	2.37	7.54	1.31	0.451	0.284	0.260	0.171	0.222
AKIM mm.	1.47	1.28	1.07	1.48	5.75	20.2	3.39	1.21	0.735	0.697	0.457	0.575
MİL. M3	3.30	2.86	2.40	3.31	12.9	45.2	7.59	2.70	1.65	1.56	1.02	1.29

SU YILI (2006) YILLIK TOPLAM AKIM 85.78 MİLYON M3 38 MM. 1.2 LT/SN/Km2

13

BATI KARADENİZ HAVZASI

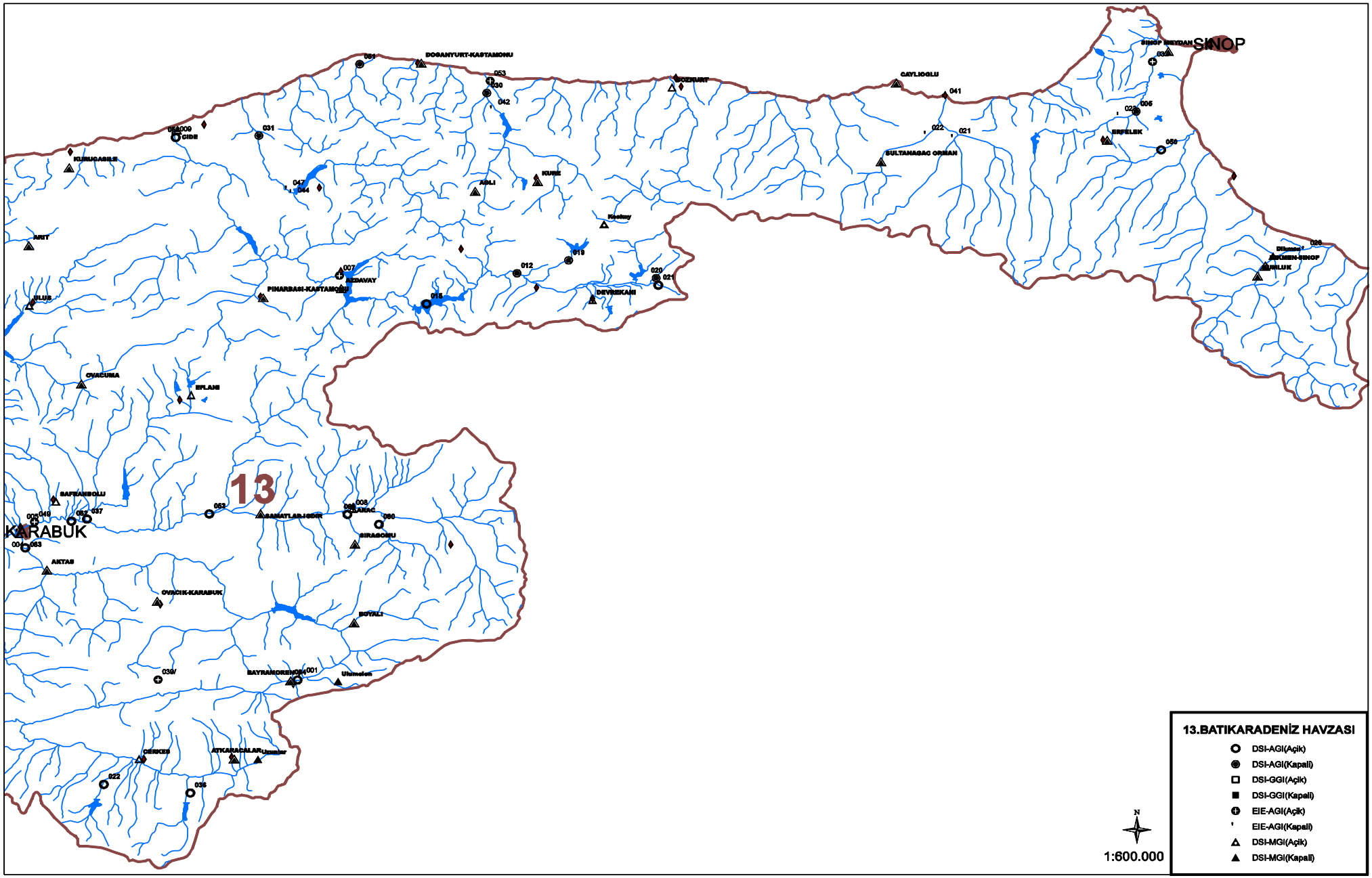

13.BATIKARADENİZ HAVZASI

- DSI-AGI(Açik)
- DSI-AGI(Kapali)
- DSI-GGI(Açik)
- DSI-GGI(Kapali)
- EIE-AGI(Açik)
- EIE-AGI(Kapali)
- DSI-MGI(Açik)
- DSI-MGI(Kapali)

N

1:600.000

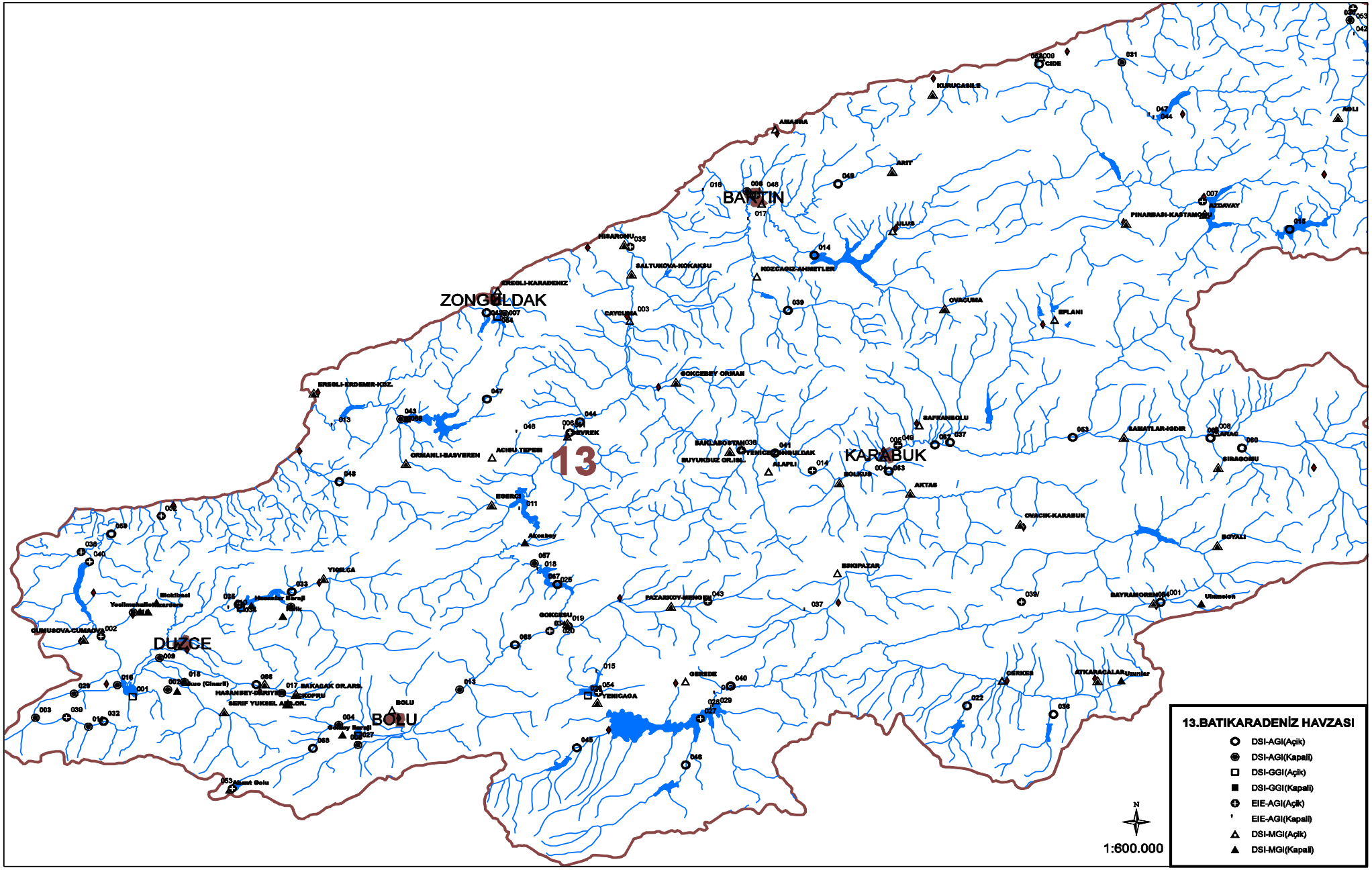
13
ZONGULDAK
KARABUK
BARTIN
DUZCE
BOLU
13.BATIKARADENİZ HAVZASI
DSI-AGI(Açik)
DSI-AGI(Kapali)
DSI-GGI(Açik)
DSI-GGI(Kapali)
EIE-AGI(Açik)
EIE-AGI(Kapali)
DSI-MGI(Açik)
DSI-MGI(Kapali)
N
1:600.000

13. Bati Karadeniz Havzasi

D13A008 MUDURNU ÇAYI AKKAYA

YERİ : **BOLU MUDURNU YOLU 8.KM ÇEPNİ KÖPRÜSÜNÜN 10 M. MANSABINDA AKMİNA TESİSLERİ İÇİNDEDİR**

31°31'35" Doğu - 40°40'47" Kuzey

YAĞIŞ ALANI : **118.30 km2** **YAKLAŞIK KOT : 749 m**

GÖZLEM SÜRESİ : **01.10.1961 - 30.09.2006**

ORTALAMA AKIMLAR : **Gözlem süresinde 1.175 m3/sn. (8 Yıllık) 2006 Su yılında 0.879 m3/sn.**

ANLIK EN ÇOK VE EN AZ AKIMLAR:

2006 Su yılında anlık ençok akım	**:**	**8.53**	**m3/sn**	**27.02.2006**
2006 Su yılında anlık enaz akım	**:**	**0.053**	**m3/sn**	**30.08.2006**
Gözlem süresinde anlık ençok akım	**:**	**52.0**	**m3/sn**	**12.03.1968**
Gözlem süresinde anlık enaz akım	**:**	**0.022**	**m3/sn**	**27.11.1967**

İstasyon için kullanılmış anahtar bulunamadı.

Akımlar 01 Ekim 2005 'den 30 Eylül 2006' a kadar m3/sn olarak

Gün	Ekim	Kasım	Aralık	Ocak	Şubat	Mart	Nisan	Mayıs	Haziran	Temmuz	Ağustos	Eylül
01	0.156	0.259	0.940	0.940	0.715	4.76	2.32	1.27	0.259	0.185	0.107	0.069
02	0.156	0.259	0.865	1.09	0.715	3.58	2.32	1.18	0.259	0.185	0.107	0.069
03	0.156	0.259	0.790	1.02	0.715	3.89	2.32	1.18	0.259	0.185	0.107	0.069
04	0.156	0.218	0.790	0.940	0.715	5.14	2.32	1.18	0.259	0.185	0.087	0.069
05	0.156	0.218	0.715	0.865	0.657	4.76	2.20	1.18	0.218	0.185	0.087	0.069
06	0.156	0.259	0.715	1.02	0.599	4.20	2.20	1.09	0.218	0.156	0.087	0.069
07	0.156	0.342	0.715	1.09	0.599	3.89	2.07	1.09	0.218	0.156	0.087	0.069
08	0.156	0.384	0.715	1.02	0.599	4.95	2.07	1.09	0.342	0.156	0.087	0.069
09	0.156	0.425	0.657	1.02	0.541	4.58	2.20	1.18	0.259	0.156	0.087	0.069
10	0.156	0.425	0.657	0.940	0.599	4.20	2.32	1.09	0.259	0.130	0.069	0.069
11	0.156	0.342	0.657	0.865	1.35	3.89	2.32	1.02	0.259	0.130	0.069	0.069
12	0.156	0.301	0.657	0.790	1.09	5.34	2.32	1.02	0.218	0.130	0.069	0.069
13	0.156	0.301	0.657	0.790	0.940	4.76	2.45	1.75	0.218	0.130	0.069	0.087
14	0.156	0.301	0.657	0.790	0.790	4.20	2.32	1.53	0.218	0.130	0.069	0.087
15	0.156	0.342	0.657	0.790	0.790	3.73	2.32	1.27	0.218	0.130	0.087	0.156
16	0.156	0.342	0.657	0.790	0.715	3.28	2.20	1.02	0.218	0.130	0.087	0.107
17	0.156	0.342	0.657	0.715	0.715	2.84	2.07	1.02	0.185	0.130	0.069	0.130
18	0.130	0.342	0.657	0.715	1.35	2.57	1.96	0.865	0.185	0.130	0.069	0.130
19	0.156	0.384	0.657	0.715	1.18	2.70	1.85	0.715	0.185	0.130	0.069	0.130
20	0.384	0.384	0.657	0.715	1.75	2.57	1.85	0.657	0.218	0.130	0.069	0.130
21	0.342	0.657	0.657	0.715	1.75	2.32	1.75	0.541	0.301	0.130	0.069	0.130
22	0.259	0.599	0.599	0.715	2.20	2.32	1.64	0.483	0.301	0.130	0.069	0.156
23	0.259	0.541	0.599	0.715	3.13	2.20	1.64	0.425	0.218	0.130	0.069	0.130
24	0.259	0.483	0.599	0.715	3.13	2.07	1.44	0.483	0.185	0.130	0.069	0.130
25	0.259	0.790	0.599	0.715	4.58	2.07	1.35	0.425	0.185	0.130	0.069	0.130
26	0.259	1.02	0.599	0.715	5.92	2.32	1.27	0.425	0.185	0.107	0.069	0.130
27	0.259	1.09	0.599	0.715	4.95	2.57	1.35	0.425	0.185	0.107	0.069	0.130
28	0.259	1.09	0.599	0.715	3.89	2.32	1.27	0.384	0.185	0.107	0.069	0.130
29	0.259	1.09	0.657	0.715	-----	2.07	1.27	0.384	0.185	0.107	0.069	0.130
30	0.259	1.02	0.657	0.715	-----	2.20	1.27	0.342	0.218	0.107	0.069	0.130
31	0.259	-----	0.715	0.715	-----	2.32	-----	0.301	-----	0.107	0.069	-----
Maks.	1.09	1.35	0.940	1.44	8.53	6.12	2.57	2.70	0.599	0.218	0.107	0.218
Min.	0.130	0.185	0.599	0.657	0.541	1.96	1.18	0.218	0.156	0.087	0.053	0.053
Ortalama	0.202	0.494	0.678	0.822	1.67	3.37	1.94	0.871	0.227	0.138	0.077	0.104
LT/SN/Km2	1.71	4.17	5.73	6.95	14.1	28.5	16.4	7.37	1.92	1.16	0.654	0.877
AKIM mm.	4.57	10.8	15.3	18.6	34.1	76.4	42.5	19.7	4.98	3.12	1.75	2.27
MİL. M3	0.540	1.28	1.82	2.20	4.03	9.04	5.03	2.33	0.589	0.369	0.207	0.269

SU YILI (2006) YILLIK TOPLAM AKIM 27.70 MİLYON M3 234 MM. 7.4 LT/SN/Km2

13. Bati Karadeniz Havzasi

D13A015 DEVREKANİ Ç. CÜRÜMÖREN

YERİ : **DADAY-AĞLI YOLUNUN 16. KM SİNDE ÇAYIRLI MEVKIINDEN AYRILAN ORMAN YOLUNUN 15. KM SINDEKI DEĞIRMENÖZÜ KÖYÜNDEDIR.**
33°29'50" Doğu - 41°35'49" Kuzey

YAĞIŞ ALANI : **729,00 km2** **YAKLAŞIK KOT : 924 m**

GÖZLEM SÜRESİ : **15.07.1965 - 30.09.2006**

ORTALAMA AKIMLAR : **Gözlem süresinde 4.134 m3/sn. (27 Yıllık) 2006 Su yılında 1.532 m3/sn.**

ANLIK EN ÇOK VE EN AZ AKIMLAR:

2006 Su yılında anlık ençok akım	**:**	**12.7**	**m3/sn**	**08.03.2006**
2006 Su yılında anlık enaz akım	**:**	**0.136**	**m3/sn**	**28.07.2006**
Gözlem süresinde anlık ençok akım	**:**	**250.**	**m3/sn**	**12.08.1971**
Gözlem süresinde anlık enaz akım	**:**	**0.002**	**m3/sn**	**05.10.1967**

100. Anahtar Eğrisi (Seviyeler cm olarak)

Seviye	Akım	Seviye	Akım	Seviye	Akım	Seviye	Akım
92	0.212	177	19.9	262	92.2	384	332.
108	1.7	193	28.9	282	119.	417	429.
125	4.0	210	40.1	304	154.	453	553.
142	7.7	227	54.2	328	199.	493	714.
159	12.8	244	71.1	355	258.	536	918.

Akımlar 01 Ekim 2005 'den 30 Eylül 2006' a kadar m3/sn olarak

Gün	Ekim	Kasım	Aralık	Ocak	Şubat	Mart	Nisan	Mayıs	Haziran	Temmuz	Ağustos	Eylül
01	0.610	1.16	2.05	1.66	1.24	1.08	3.87	1.79	0.926	0.524	0.136	0.223
02	0.524	1.16	1.92	1.79	1.08	1.08	3.74	1.79	0.926	0.524	0.136	0.438
03	0.567	1.08	1.79	1.66	1.08	1.08	3.74	1.79	0.847	0.524	0.158	0.481
04	0.610	1.08	1.79	1.66	1.08	1.08	3.61	1.79	0.847	0.524	0.158	0.481
05	0.567	1.24	1.79	1.66	1.08	1.08	3.48	1.79	0.847	0.524	0.158	0.395
06	0.567	1.24	1.79	2.05	1.08	1.08	3.22	1.79	0.768	0.524	0.136	0.395
07	0.524	1.24	1.66	2.18	1.08	4.92	3.09	1.79	0.610	0.524	0.136	0.352
08	0.524	1.24	1.40	2.18	1.08	11.7	3.09	1.92	0.689	0.524	0.158	0.352
09	0.524	1.16	1.32	2.18	1.08	11.7	3.09	1.92	0.847	0.524	0.158	0.352
10	0.524	1.08	1.32	2.18	1.16	9.06	2.96	1.79	1.01	0.524	0.158	0.352
11	0.524	0.926	1.32	2.18	1.24	8.80	2.96	1.79	1.01	0.524	0.180	0.352
12	0.524	0.926	1.24	2.18	1.24	9.06	2.96	1.79	1.08	0.524	0.158	0.352
13	0.524	0.847	1.16	2.05	1.24	9.06	2.83	2.18	1.66	0.438	0.158	0.352
14	0.524	0.847	1.16	1.79	1.24	9.06	2.44	2.96	1.92	0.352	0.158	0.309
15	0.524	1.01	1.16	1.79	1.24	9.06	2.18	3.09	1.92	0.309	0.136	0.223
16	0.524	1.40	1.08	1.53	1.08	8.55	2.18	2.57	1.66	0.309	0.136	0.223
17	0.524	1.53	1.08	1.32	1.08	8.05	2.18	2.31	1.40	0.395	0.136	0.223
18	0.524	1.24	1.16	1.32	1.08	7.80	2.18	2.18	1.40	0.481	0.136	0.180
19	0.524	1.16	1.16	1.24	1.08	7.80	2.05	2.18	1.32	0.481	0.136	0.180
20	0.610	1.16	1.16	1.32	1.08	7.80	2.05	1.79	1.16	0.395	0.136	0.180
21	0.768	1.92	1.16	1.24	1.08	6.55	2.05	1.53	1.08	0.266	0.136	0.180
22	0.926	1.92	1.08	1.16	1.08	5.84	1.92	1.40	1.01	0.223	0.136	0.180
23	0.847	1.92	1.08	1.24	1.08	5.84	1.79	1.32	0.926	0.223	0.136	0.180
24	0.847	1.79	1.08	1.24	1.08	5.84	1.79	1.24	0.926	0.223	0.136	0.180
25	0.847	1.92	1.08	1.24	1.08	5.84	1.79	1.24	0.926	0.223	0.223	0.180
26	0.689	2.05	1.08	1.24	1.08	5.61	1.79	1.24	0.768	0.223	0.223	0.266
27	0.610	2.18	1.01	1.24	1.08	5.38	1.79	1.24	0.524	0.223	0.223	0.266
28	0.610	2.18	1.01	1.24	1.08	4.92	1.79	1.24	0.524	0.158	0.223	0.266
29	0.689	2.18	1.08	1.24	-----	4.69	1.79	1.24	0.524	0.158	0.223	0.266
30	1.08	2.18	1.16	1.24	-----	4.46	1.79	1.08	0.524	0.158	0.180	0.352
31	1.16	-----	1.32	1.24	-----	4.00	-----	0.926	-----	0.158	0.180	-----
Maks.	1.16	2.18	2.18	2.18	1.40	12.7	3.87	4.23	1.92	0.524	0.223	0.481
Min.	0.481	0.847	1.01	1.08	1.01	1.08	1.79	0.926	0.524	0.136	0.136	0.180
Ortalama	0.643	1.43	1.31	1.60	1.12	6.06	2.54	1.76	1.02	0.377	0.161	0.290
LT/SN/Km2	0.882	1.96	1.80	2.19	1.53	8.31	3.48	2.42	1.40	0.517	0.220	0.398
AKIM mm.	2.36	5.09	4.82	5.86	3.71	22.3	9.03	6.48	3.62	1.38	0.590	1.03
MİL. M3	1.72	3.71	3.51	4.28	2.70	16.2	6.58	4.73	2.64	1.01	0.430	0.753

SU YILI (2006) YILLIK TOPLAM AKIM 48.26 MİLYON M3 66 MM. 2.1 LT/SN/Km2

13. Bati Karadeniz Havzasi

D13A021 DEVREKANİ Ç. ÇORBACI

YERİ : **DEVREKANİ-NASIRLI KÖYÜ YOLUNUN 11.KM SİNDEKI ÇORBACI KÖYÜNÜNDEDİR.**
33°57'27" Doğu - 41°37'36" Kuzey

YAĞIŞ ALANI : **45,50 km2** **YAKLAŞIK KOT : 1094 m**

GÖZLEM SÜRESİ : **22.07.1967 – 30.09.2006**

ORTALAMA AKIMLAR : **Gözlem süresinde 0.256 m3/sn. (29 Yıllık) 2006 Su yılında 0.212 m3/sn.**

ANLIK EN ÇOK VE EN AZ AKIMLAR:

2006 Su yılında anlık ençok akım	**:**	**1.09**	**m3/sn**	**01.03.2006**
2006 Su yılında anlık enaz akım	**:**	**0.042**	**m3/sn**	**01.08.2006**
Gözlem süresinde anlık ençok akım	**:**	**57.0**	**m3/sn**	**25.05.1987**
Gözlem süresinde anlık enaz akım	**:**	**0.000**	**m3/sn**	**09.07.1994**

Akımlar 01 Ekim 2005 'den 30 Eylül 2006' a kadar m3/sn olarak

Gün	Ekim	Kasım	Aralık	Ocak	Şubat	Mart	Nisan	Mayıs	Haziran	Temmuz	Ağustos	Eylül
01	0.184	0.209	0.234	0.209	0.234	0.697	0.356	0.234	0.209	0.158	0.070	0.053
02	0.184	0.209	0.209	0.209	0.209	0.697	0.356	0.234	0.209	0.133	0.070	0.110
03	0.184	0.209	0.209	0.209	0.209	0.641	0.356	0.234	0.209	0.133	0.070	0.110
04	0.184	0.184	0.209	0.209	0.209	0.600	0.356	0.234	0.184	0.133	0.070	0.110
05	0.158	0.184	0.209	0.209	0.209	0.600	0.315	0.234	0.184	0.133	0.070	0.086
06	0.158	0.184	0.209	0.209	0.209	0.560	0.315	0.234	0.184	0.133	0.070	0.110
07	0.158	0.184	0.209	0.234	0.209	0.560	0.315	0.275	0.184	0.133	0.070	0.110
08	0.158	0.184	0.209	0.234	0.209	0.560	0.315	0.315	0.184	0.110	0.070	0.110
09	0.158	0.184	0.209	0.209	0.209	0.519	0.315	0.315	0.209	0.110	0.053	0.110
10	0.158	0.184	0.184	0.209	0.234	0.438	0.315	0.275	0.315	0.110	0.053	0.086
11	0.158	0.184	0.184	0.209	0.234	0.560	0.315	0.275	0.356	0.110	0.053	0.086
12	0.158	0.184	0.158	0.209	0.234	0.600	0.315	0.315	0.234	0.110	0.053	0.086
13	0.158	0.184	0.158	0.209	0.234	0.641	0.315	0.356	0.209	0.110	0.053	0.086
14	0.158	0.184	0.158	0.184	0.234	0.600	0.356	0.356	0.209	0.110	0.042	0.086
15	0.184	0.158	0.158	0.184	0.209	0.560	0.356	0.356	0.209	0.110	0.042	0.086
16	0.184	0.184	0.158	0.184	0.184	0.519	0.356	0.315	0.209	0.110	0.042	0.086
17	0.184	0.184	0.158	0.184	0.184	0.519	0.315	0.275	0.209	0.110	0.042	0.086
18	0.184	0.184	0.133	0.184	0.184	0.519	0.315	0.275	0.184	0.110	0.042	0.086
19	0.209	0.184	0.158	0.158	0.184	0.478	0.315	0.275	0.184	0.086	0.042	0.086
20	0.234	0.209	0.158	0.158	0.184	0.438	0.315	0.234	0.184	0.086	0.042	0.086
21	0.234	0.234	0.158	0.158	0.209	0.438	0.275	0.234	0.184	0.086	0.053	0.086
22	0.234	0.234	0.158	0.184	0.209	0.438	0.275	0.234	0.158	0.086	0.053	0.070
23	0.234	0.234	0.158	0.184	0.209	0.438	0.275	0.234	0.184	0.086	0.042	0.070
24	0.234	0.234	0.184	0.184	0.209	0.438	0.275	0.234	0.184	0.086	0.042	0.086
25	0.234	0.209	0.184	0.184	0.234	0.438	0.275	0.234	0.184	0.086	0.042	0.133
26	0.209	0.209	0.184	0.209	0.275	0.397	0.275	0.234	0.184	0.086	0.042	0.133
27	0.209	0.209	0.184	0.234	0.315	0.397	0.275	0.209	0.184	0.070	0.042	0.133
28	0.209	0.234	0.184	0.234	0.397	0.397	0.275	0.209	0.184	0.070	0.042	0.133
29	0.234	0.234	0.184	0.234	-----	0.397	0.234	0.209	0.184	0.070	0.053	0.133
30	0.234	0.234	0.209	0.234	-----	0.397	0.234	0.209	0.184	0.070	0.053	0.133
31	0.234	-----	0.209	0.234	-----	0.397	-----	0.209	-----	0.070	0.042	-----
Maks.	0.234	0.234	0.234	0.234	0.397	1.09	0.356	0.356	0.438	0.158	0.070	0.133
Min.	0.158	0.158	0.133	0.158	0.184	0.356	0.234	0.209	0.158	0.070	0.042	0.053
Ortalama	0.193	0.201	0.183	0.202	0.224	0.512	0.309	0.260	0.202	0.103	0.052	0.099
LT/SN/Km2	4.25	4.41	4.02	4.45	4.92	11.3	6.78	5.72	4.45	2.27	1.15	2.17
AKIM mm.	11.4	11.4	10.8	11.9	11.9	30.2	17.6	15.3	11.5	6.08	3.09	5.63
MİL. M3	0.518	0.520	0.490	0.542	0.541	1.37	0.800	0.697	0.525	0.277	0.140	0.256

SU YILI (2006) YILLIK TOPLAM AKIM 6.68 MİLYON M3 147 MM. 4.7 LT/SN/Km2

13. Bati Karadeniz Havzasi

D13A022 AKHASAN DERESİ AKHASAN

YERİ : **KIZILCAHAMAM ÇERKEŞ YOLUNUN 45.KM SİNDEKİ AKHASAN KÖYÜNÜN MANSABINDADIR.**
32°48'40" Doğu - 40°46'14" Kuzey

YAĞIŞ ALANI : **76.50 km2** **YAKLAŞIK KOT : 1180 m**

GÖZLEM SÜRESİ : **15.11.1967 - 30.09.2006**

ORTALAMA AKIMLAR : **Gözlem süresinde 0.336 m3/sn. (34 Yıllık) 2006 Su yılında 0.150 m3/sn.**

ANLIK EN ÇOK VE EN AZ AKIMLAR:

2006 Su yılında anlık ençok akım	**:**	**1.24**	**m3/sn**	**24.03.2006**
2006 Su yılında anlık enaz akım	**:**	**0.001**	**m3/sn**	**12.08.2006**
Gözlem süresinde anlık ençok akım	**:**	**20.0**	**m3/sn**	**12.02.1970**
Gözlem süresinde anlık enaz akım	**:**	**0.000**	**m3/sn**	**01.08.1971**

İstasyon için kullanılmış anahtar bulunamadı.

Akımlar 01 Ekim 2005 'den 30 Eylül 2006' a kadar m3/sn olarak

Gün	Ekim	Kasım	Aralık	Ocak	Şubat	Mart	Nisan	Mayıs	Haziran	Temmuz	Ağustos	Eylül
01	0.044	0.066	0.044	0.066	0.066	0.462	0.719	0.353	0.090	0.044	0.023	0.006
02	0.044	0.066	0.044	0.066	0.066	0.462	0.719	0.353	0.090	0.044	0.023	0.006
03	0.044	0.066	0.044	0.066	0.066	0.651	0.651	0.353	0.090	0.044	0.023	0.023
04	0.044	0.066	0.044	0.066	0.066	0.516	0.651	0.353	0.090	0.044	0.023	0.023
05	0.044	0.066	0.066	0.066	0.066	0.516	0.584	0.353	0.090	0.044	0.023	0.023
06	0.044	0.066	0.066	0.066	0.066	0.516	0.516	0.245	0.090	0.044	0.023	0.023
07	0.044	0.066	0.066	0.066	0.066	0.516	0.462	0.195	0.090	0.044	0.023	0.023
08	0.044	0.066	0.066	0.066	0.066	0.462	0.516	0.245	0.090	0.044	0.023	0.006
09	0.044	0.066	0.066	0.066	0.066	0.462	0.584	0.195	0.090	0.044	0.023	0.006
10	0.044	0.066	0.066	0.066	0.066	0.516	0.651	0.195	0.090	0.044	0.023	0.006
11	0.044	0.066	0.066	0.066	0.066	0.462	0.584	0.155	0.090	0.044	0.006	0.006
12	0.044	0.066	0.066	0.066	0.066	0.462	0.516	0.155	0.090	0.044	0.001	0.006
13	0.044	0.066	0.066	0.066	0.066	0.584	0.516	0.155	0.090	0.044	0.001	0.006
14	0.044	0.066	0.066	0.066	0.066	0.719	0.516	0.155	0.090	0.044	0.001	0.023
15	0.044	0.066	0.066	0.066	0.066	0.786	0.516	0.155	0.090	0.044	0.001	0.006
16	0.044	0.066	0.066	0.066	0.066	0.719	0.462	0.155	0.090	0.044	0.001	0.006
17	0.044	0.066	0.066	0.066	0.066	0.651	0.408	0.155	0.090	0.044	0.001	0.006
18	0.044	0.066	0.066	0.066	0.066	0.516	0.408	0.155	0.090	0.044	0.001	0.006
19	0.044	0.066	0.066	0.066	0.066	0.516	0.353	0.155	0.090	0.044	0.001	0.006
20	0.044	0.066	0.066	0.066	0.090	0.516	0.299	0.155	0.090	0.023	0.001	0.006
21	0.066	0.066	0.066	0.066	0.120	0.516	0.299	0.155	0.090	0.023	0.001	0.006
22	0.044	0.066	0.066	0.066	0.120	0.516	0.353	0.155	0.090	0.023	0.001	0.006
23	0.044	0.066	0.066	0.066	0.155	0.584	0.353	0.155	0.090	0.023	0.006	0.006
24	0.044	0.066	0.066	0.066	0.245	1.01	0.353	0.155	0.090	0.044	0.006	0.006
25	0.044	0.066	0.066	0.066	0.353	0.931	0.353	0.155	0.090	0.044	0.006	0.023
26	0.044	0.066	0.066	0.066	0.408	0.786	0.353	0.155	0.090	0.044	0.006	0.023
27	0.044	0.044	0.066	0.066	0.408	0.719	0.353	0.155	0.090	0.044	0.006	0.023
28	0.066	0.044	0.066	0.066	0.408	0.719	0.353	0.155	0.090	0.044	0.006	0.023
29	0.066	0.044	0.066	0.066	-----	0.651	0.353	0.155	0.090	0.044	0.006	0.023
30	0.066	0.044	0.066	0.066	-----	0.719	0.353	0.155	0.044	0.044	0.006	0.023
31	0.066	-----	0.066	0.066	-----	0.786	-----	0.120	-----	0.023	0.006	-----
Maks.	0.090	0.090	0.090	0.090	0.651	1.24	0.786	0.353	0.195	0.120	0.044	0.044
Min.	0.023	0.023	0.023	0.044	0.044	0.408	0.299	0.120	0.044	0.006	0.001	0.006
Ortalama	0.048	0.063	0.063	0.066	0.127	0.611	0.470	0.195	0.088	0.041	0.010	0.013
LT/SN/Km2	0.622	0.824	0.826	0.863	1.66	7.99	6.15	2.56	1.16	0.531	0.127	0.167
AKIM mm.	1.66	2.14	2.21	2.31	4.02	21.4	15.9	6.84	3.00	1.42	0.340	0.434
MİL. M3	0.127	0.163	0.169	0.177	0.308	1.64	1.22	0.524	0.229	0.109	0.026	0.033

SU YILI (2006) YILLIK TOPLAM AKIM 4.73 MİLYON M3 62 MM. 2.0 LT/SN/Km2

13. Bati Karadeniz Havzasi

D13A032 AKSU DERESİ DEREEVİ

YERİ : DÜZCE-MELBUHOĞLU-BALIKLI KONAŞ KÖY YOLUNUN 27.KM SİNDEKİ DEREEVİ ORMAN İŞLEIMESİNE 600 M., MESAFEDEKİ 1000 M. MANSABINDADIR.
30°59'50" Doğu - 40°42'34" Kuzey

YAĞIŞ ALANI : 71.50 km2 YAKLAŞIK KOT : 873 m

GÖZLEM SÜRESİ : 18.11.1970 - 30.09.2006

ORTALAMA AKIMLAR : Gözlem süresinde 2.130 m3/sn. (25 Yıllık) 2006 Su yılında 1.916 m3/sn.

ANLIK EN ÇOK VE EN AZ AKIMLAR:

2006 Su yılında anlık ençok akım	:	9.52	m3/sn	27.11.2005
2006 Su yılında anlık enaz akım	:	0.345	m3/sn	31.08.2006
Gözlem süresinde anlık ençok akım	:	77.0	m3/sn	16.08.1974
Gözlem süresinde anlık enaz akım	:	0.130	m3/sn	17.10.1986

9. Anahtar Eğrisi (Seviyeler cm olarak)

Seviye	Akım	Seviye	Akım	Seviye	Akım	Seviye	Akım
15	0.100	25	0.780	50	5.4	90	20.0
17	0.180	27	0.990	55	6.8	100	24.0
19	0.290	29	1.2	60	8.4	110	28.0
21	0.415	35	2.1	70	12.0	120	32.0
23	0.580	45	4.0	80	16.0	130	36.0

Akımlar 01 Ekim 2005 'den 30 Eylül 2006' a kadar m3/sn olarak

Gün	Ekim	Kasım	Aralık	Ocak	Şubat	Mart	Nisan	Mayıs	Haziran	Temmuz	Ağustos	Eylül
01	0.550	1.17	3.96	2.19	0.950	3.30	6.09	2.54	1.06	0.670	0.415	0.415
02	0.550	1.17	3.11	2.19	0.950	3.74	6.09	2.35	1.06	0.580	0.415	0.415
03	0.550	1.30	3.74	1.88	0.950	5.55	5.82	2.35	1.06	0.580	0.415	0.415
04	0.640	1.30	3.30	1.88	0.950	5.32	5.82	2.03	0.950	0.580	0.415	0.495
05	0.640	1.88	2.92	2.54	0.950	3.96	6.09	2.19	0.950	0.580	0.415	0.495
06	0.550	3.30	2.54	2.54	0.950	3.96	5.55	2.19	0.950	0.580	0.415	0.495
07	0.550	7.21	1.88	2.19	1.06	3.52	5.82	2.19	0.950	0.580	0.415	0.495
08	0.465	4.86	1.72	2.03	1.06	3.74	7.21	2.03	0.950	0.580	0.415	0.415
09	0.550	3.30	1.72	2.19	1.06	4.40	7.52	2.03	0.950	0.580	0.415	0.415
10	0.550	2.35	1.72	1.88	1.06	3.96	6.90	2.03	0.950	0.580	0.415	0.415
11	0.550	1.88	1.72	1.72	1.06	3.52	6.90	2.54	0.950	0.495	0.415	0.415
12	0.640	1.41	1.56	1.72	0.950	3.96	8.14	2.54	0.950	0.495	0.415	0.415
13	0.640	1.17	1.56	1.56	0.950	4.40	8.81	4.40	0.950	0.495	0.415	0.415
14	0.640	1.56	1.41	2.35	0.950	4.40	8.14	3.52	0.950	0.495	0.415	0.345
15	0.640	1.72	1.41	2.35	0.950	4.63	7.21	3.30	0.950	0.495	0.415	0.345
16	0.740	1.56	1.17	2.35	1.06	4.63	6.36	3.11	0.950	0.495	0.415	0.345
17	1.30	1.41	1.06	1.88	1.06	4.18	5.55	2.35	0.950	0.495	0.415	0.345
18	0.950	2.19	1.06	1.41	1.06	3.96	5.09	1.88	0.840	0.495	0.415	0.345
19	0.840	2.35	1.17	1.17	1.06	3.30	4.86	1.88	0.840	0.495	0.415	0.345
20	0.740	2.92	1.30	2.03	1.17	2.92	4.86	1.72	0.840	0.495	0.415	0.345
21	1.72	2.73	1.30	1.72	1.72	2.92	4.40	1.56	0.840	0.415	0.415	0.415
22	1.30	3.11	1.17	1.41	1.88	2.54	3.74	1.56	0.740	0.415	0.415	0.415
23	1.17	2.73	1.06	1.17	2.19	2.54	3.30	1.56	0.740	0.415	0.415	0.415
24	0.950	3.52	1.30	2.35	2.19	3.30	2.54	1.41	0.740	0.415	0.415	0.415
25	0.950	3.96	1.17	2.35	2.35	4.86	2.54	1.41	0.740	0.415	0.415	0.415
26	0.950	6.09	1.17	2.92	2.73	6.90	2.54	1.30	0.740	0.415	0.415	0.415
27	0.840	7.52	1.17	2.54	4.18	5.32	2.35	1.30	0.740	0.415	0.415	0.415
28	0.840	7.21	0.950	2.54	3.74	5.32	2.35	1.17	0.840	0.415	0.415	0.415
29	0.950	5.82	1.17	2.35	-----	5.32	2.54	1.17	1.30	0.415	0.415	0.415
30	1.17	4.40	1.30	2.19	-----	5.09	2.73	1.17	1.36	0.415	0.415	0.495
31	1.41	-----	2.35	1.88	-----	6.09	-----	1.17	-----	0.415	0.415	-----
Maks.	2.35	9.52	4.63	3.52	5.32	7.83	9.52	7.52	1.88	0.670	0.415	0.880
Min.	0.465	0.950	0.950	1.06	0.840	2.35	2.19	1.06	0.740	0.415	0.345	0.345
Ortalama	0.823	3.10	1.75	2.05	1.47	4.24	5.26	2.06	0.926	0.497	0.415	0.412
LT/SN/Km2	11.5	43.4	24.4	28.6	20.6	59.4	73.6	28.9	13.0	6.95	5.80	5.76
AKIM mm.	30.8	113.	65.4	76.7	49.8	159.	191.	77.3	33.6	18.6	15.5	14.9
MİL. M3	2.21	8.04	4.68	5.48	3.56	11.4	13.6	5.53	2.40	1.33	1.11	1.07

SU YILI (2006) YILLIK TOPLAM AKIM 60.41 MİLYON M3 845 MM. 26.8 LT/SN/Km2

13. Bati Karadeniz Havzasi

D13A033 KÜÇÜK MELEN DERESİ İĞNELER

YERİ : DÜZCE YIĞILCA YOLUNUN 26.KM SİNDEKİ İĞNELER KÖYÜNÜN 1 KM. MANSABINDADIR.
32°23'22" Doğu - 40°56'25" Kuzey

YAĞIŞ ALANI : 259.70 km2 YAKLAŞIK KOT : 276 m

GÖZLEM SÜRESİ : 06.09.1971 - 30.09.2006

ORTALAMA AKIMLAR : Gözlem süresinde 6.040 m3/sn. (26 Yıllık) 2006 Su yılında 4.861 m3/sn.

ANLIK EN ÇOK VE EN AZ AKIMLAR:

2006 Su yılında anlık ençok akım	:	117.	m3/sn	25.11.2005
2006 Su yılında anlık enaz akım	:	0.280	m3/sn	11.07.2006
Gözlem süresinde anlık ençok akım	:	510.	m3/sn	28.08.1982
Gözlem süresinde anlık enaz akım	:	0.000	m3/sn	01.09.1986

5. Anahtar Eğrisi (Seviyeler cm olarak)

Seviye	Akım	Seviye	Akım	Seviye	Akım	Seviye	Akım
12	0.325	30	2.0	100	39.0	160	98.5
14	0.440	40	3.8	120	56.0	170	110.
16	0.565	50	6.2	130	66.0	180	122.
18	0.710	60	10.6	140	76.5	190	135.
20	0.875	80	24.0	150	87.0	200	148.

Akımlar 01 Ekim 2005 'den 30 Eylül 2006' a kadar m3/sn olarak

Gün	Ekim	Kasım	Aralık	Ocak	Şubat	Mart	Nisan	Mayıs	Haziran	Temmuz	Ağustos	Eylül
01	0.710	3.05	4.51	19.1	2.37	17.0	4.66	1.99	1.30	0.660	0.280	0.590
02	0.710	2.53	3.65	9.25	3.05	14.2	4.22	1.86	1.30	0.590	0.280	0.460
03	0.875	2.05	3.45	7.09	3.25	35.8	4.22	1.86	1.30	0.590	0.280	0.400
04	1.53	1.92	2.85	6.67	3.65	26.1	4.00	1.60	1.20	0.590	0.340	0.400
05	1.79	2.05	5.21	6.67	3.85	17.5	3.80	1.60	1.20	0.520	0.340	0.400
06	1.19	4.73	4.29	6.67	3.45	13.7	3.60	1.60	1.20	0.520	0.340	0.400
07	1.19	10.2	3.05	12.5	3.05	12.0	3.40	1.99	1.00	0.520	0.340	0.400
08	1.19	7.51	2.53	12.5	2.85	13.1	3.60	1.73	1.00	0.460	0.340	0.400
09	1.19	4.51	2.69	7.09	2.69	12.0	3.60	2.25	1.00	0.460	0.340	0.400
10	1.19	3.25	2.37	5.21	4.95	10.7	3.40	2.12	1.00	0.400	0.340	0.400
11	1.19	2.69	2.05	4.07	36.6	14.2	3.20	1.99	1.30	0.340	0.340	0.400
12	1.19	2.37	1.79	3.45	11.2	25.4	3.00	1.99	1.10	0.340	0.340	0.400
13	1.53	2.21	1.66	3.05	5.99	19.5	3.00	1.73	1.10	0.340	0.340	0.400
14	1.30	2.53	1.53	2.85	4.95	13.7	2.85	2.25	1.50	0.340	0.400	0.400
15	1.40	3.45	1.53	2.53	4.07	10.7	2.85	1.86	1.30	0.340	0.400	0.400
16	1.30	3.25	2.53	2.21	3.65	8.36	2.70	1.60	1.20	0.340	0.400	0.400
17	1.30	2.69	5.73	2.21	3.45	7.36	2.55	1.40	1.10	0.340	0.400	0.400
18	1.30	3.05	3.65	2.05	7.93	6.40	2.40	1.30	1.00	0.340	0.400	0.400
19	2.53	3.25	3.65	2.21	28.2	7.36	2.40	1.30	1.00	0.340	0.400	0.400
20	57.0	11.2	3.25	2.53	34.2	7.04	2.25	1.30	1.00	0.340	0.400	0.400
21	17.7	18.4	3.05	2.37	28.9	6.72	2.25	1.30	0.900	0.340	0.400	0.460
22	4.73	9.25	2.85	2.37	24.7	6.72	2.25	1.30	0.900	0.340	0.400	0.460
23	3.25	7.93	3.05	2.53	22.1	7.04	2.12	1.30	0.740	0.340	0.400	0.460
24	3.05	67.1	3.05	2.37	18.8	7.68	2.12	1.30	0.740	0.340	0.460	0.460
25	2.69	89.3	3.05	2.21	20.1	6.72	2.12	1.30	0.740	0.340	0.460	0.460
26	2.21	61.0	3.05	2.21	28.2	5.62	1.99	1.30	0.660	0.340	0.400	0.460
27	1.92	31.8	3.85	2.05	23.4	5.10	1.99	1.30	0.660	0.340	0.400	0.590
28	1.66	18.4	27.5	2.05	17.5	4.88	1.99	1.30	0.660	0.340	0.400	0.520
29	1.66	10.2	30.3	1.92	-----	4.88	1.99	1.30	0.660	0.340	0.400	0.520
30	1.66	6.25	21.2	2.05	-----	5.10	1.99	1.30	0.660	0.340	0.400	0.660
31	2.37	-----	26.1	2.21	-----	4.66	-----	1.30	-----	0.340	0.400	-----
Maks.	78.6	117.	43.0	31.0	61.0	79.7	4.66	3.00	2.70	0.660	0.520	0.820
Min.	0.710	1.92	1.40	1.79	2.21	4.44	1.99	1.20	0.590	0.280	0.280	0.340
Ortalama	4.02	13.3	6.10	4.65	12.8	11.5	2.88	1.60	1.01	0.402	0.373	0.443
LT/SN/Km2	15.5	51.1	23.5	17.9	49.1	44.4	11.1	6.16	3.90	1.55	1.44	1.71
AKIM mm.	41.4	132.	62.9	48.0	119.	119.	28.8	16.5	10.1	4.14	3.85	4.42
MİL. M3	10.8	34.4	16.3	12.5	30.9	30.9	7.47	4.29	2.63	1.08	0.999	1.15

SU YILI (2006) YILLIK TOPLAM AKIM 153.42 MİLYON M3 591 MM. 18.7 LT/SN/Km2

13. Bati Karadeniz Havzasi

D13A036 HACILAR DERESİ YALAKÖZÜ

YERİ : ÇERKEŞ-KURŞUNLU YOLUNUN 13.KM SİNDEKİ YALAKÖZÜ KÖYÜNÜN 200 M. MANSABINDADIR.
32°59'27" Doğu - 40°45'43" Kuzey

YAĞIŞ ALANI : 88.30 km2 **YAKLAŞIK KOT :** 1179 m

GÖZLEM SÜRESİ : 17.11.1971 - 30.09.2006

ORTALAMA AKIMLAR : Gözlem süresinde 0.645 m3/sn. (31 Yıllık) 2006 Su yılında 0.301 m3/sn.

ANLIK EN ÇOK VE EN AZ AKIMLAR:

2006 Su yılında anlık ençok akım	:	3.90	m3/sn	23.03.2006
2006 Su yılında anlık enaz akım	:	0.034	m3/sn	30.05.2006
Gözlem süresinde anlık ençok akım	:	120.	m3/sn	12.05.1975
Gözlem süresinde anlık enaz akım	:	0.000	m3/sn	09.01.1972

10. Anahtar Eğrisi (Seviyeler cm olarak)

Seviye	Akım	Seviye	Akım	Seviye	Akım	Seviye	Akım
3	0.003	13	0.480	50	7.0	100	20.0
5	0.034	15	0.655	60	9.2	110	23.5
7	0.100	25	1.8	70	11.5	120	27.0
9	0.200	30	2.6	80	14.2	130	31.0
11	0.325	40	4.8	90	17.0	140	35.0

Akımlar 01 Ekim 2005 'den 30 Eylül 2006' a kadar m3/sn olarak

Gün	Ekim	Kasım	Aralık	Ocak	Şubat	Mart	Nisan	Mayıs	Haziran	Temmuz	Ağustos	Eylül
01	0.070	0.070	0.200	0.145	0.200	0.480	1.56	0.400	0.034	0.064	0.064	0.034
02	0.070	0.070	0.200	0.145	0.200	0.560	1.56	0.400	0.034	0.064	0.064	0.034
03	0.070	0.070	0.145	0.145	0.200	1.06	1.29	0.400	0.034	0.064	0.064	0.034
04	0.070	0.070	0.145	0.145	0.200	1.82	1.16	0.400	0.064	0.064	0.064	0.034
05	0.070	0.145	0.145	0.145	0.200	1.56	1.06	0.400	0.064	0.064	0.064	0.034
06	0.070	0.145	0.145	0.145	0.145	1.69	0.958	0.325	0.064	0.064	0.064	0.034
07	0.070	0.145	0.145	0.200	0.145	2.14	0.958	0.325	0.064	0.064	0.064	0.034
08	0.070	0.145	0.145	0.200	0.145	2.14	0.958	0.325	0.064	0.064	0.064	0.034
09	0.070	0.145	0.145	0.145	0.145	1.82	1.06	0.325	0.064	0.064	0.064	0.034
10	0.070	0.145	0.145	0.145	0.145	1.42	1.06	0.325	0.064	0.064	0.034	0.034
11	0.070	0.145	0.145	0.145	0.200	1.16	0.958	0.325	0.100	0.064	0.034	0.034
12	0.070	0.145	0.145	0.145	0.200	1.16	0.857	0.325	0.100	0.064	0.034	0.034
13	0.070	0.145	0.145	0.145	0.200	1.69	0.857	0.325	0.100	0.064	0.034	0.034
14	0.070	0.145	0.145	0.145	0.200	2.14	0.857	0.325	0.100	0.064	0.034	0.034
15	0.070	0.145	0.145	0.145	0.200	1.98	0.756	0.325	0.100	0.064	0.034	0.034
16	0.070	0.145	0.145	0.145	0.200	1.56	0.756	0.325	0.100	0.064	0.034	0.034
17	0.070	0.145	0.145	0.145	0.200	1.56	0.560	0.325	0.100	0.064	0.034	0.034
18	0.070	0.145	0.145	0.145	0.200	1.16	0.560	0.325	0.100	0.064	0.034	0.034
19	0.070	0.145	0.145	0.145	0.200	0.958	0.560	0.200	0.100	0.064	0.034	0.034
20	0.070	0.145	0.145	0.145	0.200	0.857	0.560	0.200	0.100	0.064	0.034	0.034
21	0.070	0.145	0.145	0.145	0.260	0.857	0.560	0.200	0.064	0.064	0.034	0.034
22	0.070	0.145	0.145	0.145	0.260	1.06	0.560	0.200	0.064	0.064	0.034	0.034
23	0.070	0.145	0.145	0.145	0.325	2.14	0.560	0.200	0.064	0.064	0.034	0.064
24	0.070	0.145	0.145	0.145	0.325	3.26	0.560	0.200	0.064	0.064	0.034	0.064
25	0.070	0.145	0.145	0.145	0.325	2.83	0.480	0.145	0.064	0.064	0.034	0.100
26	0.070	0.145	0.145	0.200	0.400	1.98	0.400	0.100	0.064	0.064	0.034	0.100
27	0.070	0.145	0.145	0.145	0.400	1.69	0.400	0.100	0.064	0.064	0.034	0.100
28	0.070	0.145	0.145	0.200	0.325	1.56	0.400	0.064	0.064	0.064	0.034	0.100
29	0.070	0.145	0.145	0.145	-----	1.56	0.400	0.064	0.064	0.064	0.034	0.100
30	0.070	0.145	0.145	0.145	-----	1.56	0.400	0.034	0.100	0.064	0.034	0.100
31	0.070	-----	0.145	0.200	-----	1.82	-----	0.034	-----	0.064	0.034	-----
Maks.	0.070	0.200	0.200	0.200	0.560	3.90	1.82	0.560	0.100	0.100	0.064	0.145
Min.	0.041	0.070	0.100	0.145	0.145	0.480	0.400	0.034	0.034	0.064	0.034	0.034
Ortalama	0.070	0.135	0.149	0.154	0.227	1.59	0.787	0.257	0.074	0.064	0.043	0.049
LT/SN/Km2	0.793	1.53	1.68	1.74	2.57	18.0	8.92	2.91	0.840	0.725	0.484	0.557
AKIM mm.	2.12	3.96	4.51	4.67	6.21	48.2	23.1	7.79	2.18	1.94	1.30	1.44
MİL. M3	0.187	0.350	0.398	0.412	0.548	4.25	2.04	0.688	0.192	0.171	0.114	0.128

SU YILI (2006) YILLIK TOPLAM AKIM 9.48 MİLYON M3 107 MM. 3.4 LT/SN/Km2

13. Bati Karadeniz Havzasi

D13A037 EFLANİ Ç. ÇEVRİKKÖPRÜ

YERİ : SAFRANBOLU-KASTAMONU KARAYOLUNUN 8. KM.SİNDEKİ ÇEVRİKKÖPRÜ'NÜN 500 M MEMBAINDADIR
32°45'50" Doğu - 41°13'7" Kuzey

YAĞIŞ ALANI : 537,10 km2 YAKLAŞIK KOT : 322 m

GÖZLEM SÜRESİ : 26.10.1971 - 30.09.2006

ORTALAMA AKIMLAR : Gözlem süresinde 3.611 m3/sn. (30 Yıllık) 2006 Su yılında 2.926 m3/sn.

ANLIK EN ÇOK VE EN AZ AKIMLAR:

2006 Su yılında anlık ençok akım	:	53.2	m3/sn	27.02.2006
2006 Su yılında anlık enaz akım	:	0.005	m3/sn	26.08.2006
Gözlem süresinde anlık ençok akım	:	272.	m3/sn	21.05.1998
Gözlem süresinde anlık enaz akım	:	0.000	m3/sn	10.03.1994

6. Anahtar Eğrisi (Seviyeler cm olarak)

Seviye	Akım	Seviye	Akım	Seviye	Akım	Seviye	Akım
64	0.010	130	9.2	230	39.0	330	68.0
74	0.280	150	14.5	250	46.0	350	75.0
84	1.1	170	20.0	270	51.0	370	84.0
94	2.0	190	26.0	290	57.0	390	90.0
110	4.8	210	32.0	310	62.0	400	92.0

Akımlar 01 Ekim 2005 'den 30 Eylül 2006' a kadar m3/sn olarak

Gün	Ekim	Kasım	Aralık	Ocak	Şubat	Mart	Nisan	Mayıs	Haziran	Temmuz	Ağustos	Eylül
01	0.252	0.408	1.54	5.45	1.90	39.8	3.52	1.23	0.524	0.276	0.027	0.010
02	0.276	0.408	1.38	4.33	1.90	39.8	3.26	1.30	0.524	0.300	0.018	0.010
03	0.276	0.444	1.38	3.76	1.62	37.4	3.26	1.16	0.480	0.228	0.018	0.014
04	0.276	0.444	1.30	3.40	1.62	34.7	2.98	1.08	0.480	0.180	0.018	0.014
05	0.276	0.480	1.30	3.40	1.70	26.3	2.84	1.01	0.444	0.180	0.018	0.010
06	0.252	0.524	1.62	5.60	1.80	21.8	2.70	1.01	0.444	0.130	0.018	0.010
07	0.252	0.524	1.46	8.56	1.80	19.5	2.50	1.01	0.408	0.155	0.014	0.010
08	0.228	0.568	1.38	9.76	1.90	18.8	2.50	1.08	0.408	0.155	0.014	0.010
09	0.228	0.612	1.30	7.20	1.90	18.5	2.40	1.08	0.408	0.204	0.014	0.010
10	0.204	0.568	1.38	5.80	2.20	14.5	2.30	1.16	0.524	0.180	0.018	0.010
11	0.204	0.568	1.16	5.15	5.15	13.5	2.20	1.16	0.524	0.180	0.014	0.018
12	0.228	0.524	1.08	4.33	5.80	15.4	2.10	1.08	0.568	0.130	0.010	0.018
13	0.252	0.480	1.08	3.88	5.00	15.4	2.00	1.54	0.568	0.130	0.010	0.014
14	0.252	0.480	1.01	3.64	4.33	13.8	1.90	1.70	0.700	0.130	0.010	0.014
15	0.252	0.524	1.01	3.26	4.00	12.3	1.90	1.46	0.748	0.130	0.010	0.014
16	0.252	0.612	1.01	2.98	3.76	10.8	1.80	1.23	0.656	0.111	0.010	0.010
17	0.252	0.656	1.16	2.84	3.52	9.76	1.70	1.16	0.568	0.111	0.010	0.010
18	0.252	0.656	1.30	2.70	4.17	9.04	1.62	1.08	0.524	0.111	0.010	0.010
19	0.300	0.612	1.38	2.60	13.3	9.04	1.54	0.940	0.480	0.092	0.007	0.010
20	0.748	0.656	1.46	2.70	20.0	8.32	1.54	0.892	0.444	0.078	0.010	0.010
21	0.844	1.08	1.46	2.40	20.0	7.60	1.54	0.844	0.408	0.064	0.010	0.010
22	0.700	1.16	1.46	2.40	21.2	7.00	1.46	0.844	0.372	0.050	0.010	0.010
23	0.656	1.30	1.54	2.40	20.9	6.40	1.38	0.796	0.336	0.064	0.010	0.010
24	0.524	1.46	1.54	2.20	20.6	6.20	1.38	0.796	0.300	0.064	0.007	0.007
25	0.480	1.70	1.54	2.20	21.2	6.00	1.38	0.700	0.300	0.050	0.007	0.010
26	0.444	2.10	1.46	2.40	33.2	5.45	1.30	0.700	0.276	0.035	0.005	0.010
27	0.408	2.50	1.46	2.10	45.2	4.83	1.23	0.700	0.276	0.035	0.007	0.010
28	0.372	2.30	1.62	2.00	39.5	4.50	1.16	0.700	0.276	0.035	0.010	0.014
29	0.408	1.90	2.84	1.80	-----	4.17	1.16	0.700	0.300	0.027	0.014	0.014
30	0.372	1.62	3.26	1.80	-----	4.00	1.16	0.656	0.300	0.027	0.014	0.010
31	0.372	-----	3.76	1.62	-----	3.88	-----	0.568	-----	0.027	0.010	-----
Maks.	0.892	2.60	3.76	10.4	53.2	46.0	3.64	1.80	0.796	0.300	0.035	0.027
Min.	0.204	0.372	1.01	1.54	1.54	3.76	1.08	0.568	0.252	0.027	0.005	0.007
Ortalama	0.358	0.929	1.54	3.70	11.0	14.5	1.99	1.01	0.452	0.118	0.012	0.011
LT/SN/Km2	0.666	1.73	2.86	6.89	20.6	26.9	3.71	1.88	0.842	0.220	0.023	0.021
AKIM mm.	1.78	4.48	7.66	18.4	49.7	72.1	9.61	5.05	2.18	0.590	0.061	0.055
MİL. M3	0.958	2.41	4.12	9.91	26.7	38.7	5.16	2.71	1.17	0.317	0.033	0.029

SU YILI (2006) YILLIK TOPLAM AKIM 92.22 MİLYON M3 172 MM. 5.4 LT/SN/Km2

13. Bati Karadeniz Havzasi

D13A038 KARA DERE KIRIK

YERİ : **DÜZCE-YIĞILCA YOLU 26.KM SİNDEKİ İĞNELER KÖYÜNDEN SAĞA DÖNÜLDÜĞÜNDE KARADERE YOLUNUN 7. KM SİNDE KIRIK KÖYÜNDEDİR.**
31°23'8" Doğu - 40°55'2" Kuzey

YAĞIŞ ALANI : **225.90 km2** **YAKLAŞIK KOT : 311 m**

GÖZLEM SÜRESİ : **01.11.1973 - 30.09.2006**

ORTALAMA AKIMLAR : **Gözlem süresinde 4.116 m3/sn. (10 Yıllık) 2006 Su yılında 3.825 m3/sn.**

ANLIK EN ÇOK VE EN AZ AKIMLAR:

2006 Su yılında anlık ençok akım	:	**28.6**	**m3/sn**	**26.11.2005**
2006 Su yılında anlık enaz akım	:	**0.940**	**m3/sn**	**16.08.2006**
Gözlem süresinde anlık ençok akım	:	**175.**	**m3/sn**	**01.05.1975**
Gözlem süresinde anlık enaz akım	:	**0.012**	**m3/sn**	**31.05.1975**

İstasyon için kullanılmış anahtar bulunamadı.

Akımlar 01 Ekim 2005 'den 30 Eylül 2006' a kadar m3/sn olarak

Gün	Ekim	Kasım	Aralık	Ocak	Şubat	Mart	Nisan	Mayıs	Haziran	Temmuz	Ağustos	Eylül
01	1.09	1.92	6.16	12.7	3.75	12.2	4.89	2.62	1.75	1.51	1.09	1.34
02	1.09	1.75	5.13	10.1	3.88	10.8	4.77	2.53	1.75	1.51	1.09	1.18
03	1.09	1.58	4.65	8.28	4.01	16.0	4.54	2.53	1.66	1.69	1.09	1.09
04	1.51	1.41	4.10	7.76	4.27	16.5	4.43	2.44	1.66	1.51	1.01	1.01
05	1.78	1.75	4.65	8.10	4.53	14.0	4.32	2.44	1.58	1.42	1.01	1.01
06	1.26	3.00	4.21	8.10	4.66	12.0	4.10	2.36	1.58	1.42	1.01	0.940
07	1.09	4.65	3.90	8.28	4.66	10.8	4.00	2.44	1.66	1.34	1.01	0.940
08	1.09	4.21	3.60	7.76	4.40	10.8	4.00	2.44	1.75	1.34	1.01	0.940
09	1.01	3.40	3.60	6.93	4.14	9.86	4.10	3.60	2.01	1.34	1.01	0.940
10	1.01	2.81	3.30	6.31	5.33	8.70	4.00	2.81	2.18	1.34	1.01	0.940
11	1.01	2.36	3.10	5.75	9.36	9.02	3.80	2.53	2.18	1.26	1.01	0.940
12	1.01	2.09	3.00	5.19	7.42	11.5	3.80	2.44	2.09	1.18	1.01	0.940
13	1.69	2.01	2.81	4.92	6.17	12.6	3.80	3.60	1.84	1.18	1.01	0.940
14	1.26	2.18	2.72	4.66	5.47	11.3	3.70	3.10	2.62	1.18	1.01	0.940
15	1.42	2.18	2.72	4.27	4.92	9.86	3.60	2.72	2.35	1.18	1.01	0.940
16	1.34	2.09	3.10	4.01	4.66	8.70	3.40	2.62	2.45	1.09	0.940	0.940
17	1.26	2.01	3.40	3.88	4.53	7.63	3.30	2.44	2.06	1.09	0.940	0.940
18	2.06	2.36	3.10	3.75	5.75	6.96	3.20	2.36	1.87	1.09	0.940	0.940
19	1.69	2.18	3.40	4.14	11.4	6.96	3.10	2.27	1.78	1.09	0.940	0.940
20	2.35	3.50	3.20	4.40	16.9	6.42	3.10	2.18	1.78	1.09	0.940	0.940
21	10.9	4.77	2.91	4.01	16.9	6.42	3.00	2.09	1.69	1.09	0.940	1.18
22	5.25	3.80	2.91	4.01	16.9	6.16	3.00	2.09	1.69	1.09	0.940	1.09
23	3.10	4.00	3.00	4.14	16.4	6.55	2.91	2.01	1.69	1.09	0.940	0.940
24	2.53	15.8	3.00	3.88	15.7	7.36	2.81	2.01	1.69	1.09	0.940	1.26
25	2.81	20.4	2.91	3.75	16.4	6.96	2.72	2.01	1.60	1.09	0.940	1.42
26	2.72	23.4	3.10	3.75	16.0	6.16	2.72	2.01	1.60	1.09	0.940	1.09
27	2.27	18.4	3.40	3.64	15.1	5.64	2.72	2.01	1.60	1.09	0.940	0.940
28	1.84	14.9	6.03	3.53	13.1	5.25	2.72	2.01	1.97	1.09	0.940	0.940
29	1.66	10.4	8.70	3.20	-----	5.13	2.72	1.92	1.60	1.09	0.940	0.940
30	1.75	7.77	9.02	3.20	-----	5.13	2.72	1.84	1.60	1.09	0.940	1.26
31	1.66	-----	10.8	3.53	-----	5.13	-----	1.84	-----	1.09	0.940	-----
Maks.	15.1	28.6	13.3	15.0	17.6	24.0	5.25	4.65	3.50	2.25	1.09	2.15
Min.	1.01	1.41	2.62	2.65	3.53	4.89	2.53	1.66	1.51	1.09	0.940	0.940
Ortalama	2.05	5.77	4.18	5.48	8.81	8.98	3.53	2.40	1.84	1.22	0.982	1.03
LT/SN/Km2	9.08	25.5	18.5	24.3	39.0	39.8	15.6	10.6	8.16	5.40	4.35	4.54
AKIM mm.	24.3	66.2	49.6	65.0	94.4	107.	40.5	28.4	21.2	14.5	11.6	11.8
MİL. M3	5.50	15.0	11.2	14.7	21.3	24.1	9.16	6.42	4.78	3.27	2.63	2.66

SU YILI (2006) YILLIK TOPLAM AKIM 120.72 MİLYON M3 534 MM. 16.9 LT/SN/Km2

13. Bati Karadeniz Havzasi

D13A039 KOCANAZ Ç. BOĞAZKÖY

YERİ : BARTIN-KOCANAZ ORMAN YOLUNUN 35.KM SİNDE BOĞAZKÖY'DEDİR.
32°22'45" Doğu - 41°27'48" Kuzey

YAĞIŞ ALANI : 332,00 km2 YAKLAŞIK KOT : 130 m

GÖZLEM SÜRESİ : 20.09.1974 - 30.09.2006

ORTALAMA AKIMLAR : Gözlem süresinde 5.285 m3/sn. (23 Yıllık) 2006 Su yılında 4.420 m3/sn.

ANLIK EN ÇOK VE EN AZ AKIMLAR:

2006 Su yılında anlık ençok akım	:	42.4	m3/sn	11.02.2006
2006 Su yılında anlık enaz akım	:	0.028	m3/sn	10.07.2006
Gözlem süresinde anlık ençok akım	:	210.	m3/sn	27.12.1985
Gözlem süresinde anlık enaz akım	:	0.028	m3/sn	10.07.2006

2011. Anahtar Eğrisi (Seviyeler cm olarak)

Seviye	Akım	Seviye	Akım	Seviye	Akım	Seviye	Akım
22	0.001	66	5.7	112	22.0	185	49.2
30	0.065	75	8.5	122	25.9	207	56.7
39	0.443	84	11.7	133	30.3	234	65.4
48	1.5	93	15.1	146	35.3	266	75.1
57	3.3	102	18.4	162	41.0	305	86.0

Akımlar 01 Ekim 2005 'den 30 Eylül 2006' a kadar m3/sn olarak

Gün	Ekim	Kasım	Aralık	Ocak	Şubat	Mart	Nisan	Mayıs	Haziran	Temmuz	Ağustos	Eylül
01	0.120	6.16	5.80	15.9	4.79	15.9	6.16	0.868	0.227	0.110	0.045	0.441
02	0.120	5.13	4.12	10.1	5.80	16.6	6.16	0.815	0.173	0.100	0.086	1.02
03	0.173	3.10	4.45	6.88	5.13	27.3	6.16	0.654	0.120	0.086	0.120	0.601
04	0.387	1.65	4.12	6.16	4.79	21.4	5.80	0.601	0.173	0.073	0.120	0.494
05	0.280	1.96	13.0	5.80	4.79	12.3	5.46	0.601	0.173	0.059	0.120	0.387
06	0.173	3.78	8.32	7.96	5.13	10.1	4.79	0.601	0.120	0.045	0.120	0.387
07	0.120	6.88	5.46	13.7	6.16	9.40	4.79	0.601	0.110	0.037	0.173	0.334
08	0.120	7.60	7.92	19.5	5.13	8.68	6.16	0.761	0.110	0.037	0.120	0.280
09	0.110	6.16	9.88	13.0	5.13	12.3	6.88	3.78	0.110	0.037	0.120	0.227
10	0.110	3.44	7.04	8.32	6.88	11.6	5.46	4.12	0.387	0.028	0.120	0.173
11	0.110	2.27	5.40	6.88	30.4	12.3	5.13	2.12	0.387	0.028	0.120	0.227
12	0.227	1.34	4.60	5.80	15.9	13.7	5.46	1.49	0.547	0.045	0.173	0.227
13	0.280	1.02	3.96	5.13	9.40	13.0	5.80	3.10	0.494	0.073	0.173	0.173
14	0.334	1.18	3.32	4.12	10.1	12.3	5.13	3.44	1.49	0.073	0.173	0.120
15	0.334	1.96	3.32	3.10	7.24	9.40	4.12	2.27	0.761	0.073	0.173	0.120
16	0.761	1.65	4.28	2.43	6.52	8.32	3.44	1.49	0.387	0.073	0.173	0.120
17	1.81	1.34	12.2	2.27	6.16	7.60	2.43	1.02	0.280	0.059	0.173	0.120
18	1.81	1.65	10.4	2.12	15.2	6.88	2.12	0.815	0.227	0.059	0.173	0.120
19	2.43	1.65	18.0	2.43	34.4	8.32	1.96	0.654	0.173	0.059	0.173	0.120
20	27.3	4.79	15.0	5.46	31.4	6.88	1.81	0.547	0.120	0.059	0.173	0.120
21	7.96	14.4	11.5	5.46	25.3	6.16	1.65	0.547	0.120	0.059	0.173	0.227
22	4.12	8.68	9.34	4.79	19.5	5.46	1.49	0.494	0.110	0.045	0.173	0.547
23	2.12	7.24	8.80	5.80	16.6	6.16	1.18	0.441	0.110	0.045	0.173	0.441
24	1.96	16.6	7.92	4.79	15.2	8.32	0.868	0.387	0.100	0.059	0.173	0.387
25	2.43	28.4	7.48	3.78	15.9	8.68	0.815	0.334	0.100	0.059	0.173	0.441
26	2.43	23.4	7.92	3.78	22.4	7.24	0.761	0.334	0.086	0.045	0.227	0.654
27	2.43	15.9	9.34	3.44	17.6	6.52	0.708	0.547	0.100	0.045	0.227	0.494
28	3.78	13.0	28.7	2.43	13.0	5.80	0.654	0.494	0.334	0.045	0.173	0.387
29	4.45	9.04	15.9	2.27	-----	5.80	0.601	0.387	0.227	0.045	0.173	0.441
30	4.45	7.60	12.3	2.77	-----	6.16	0.601	0.334	0.120	0.045	0.173	5.13
31	3.78	-----	16.6	2.77	-----	6.16	-----	0.280	-----	0.037	0.173	-----
Maks.	33.4	30.4	33.9	24.3	42.4	39.4	7.24	7.60	2.12	0.110	0.227	7.60
Min.	0.100	0.868	3.00	1.96	3.44	5.13	0.547	0.227	0.086	0.028	0.045	0.120
Ortalama	2.48	6.97	9.24	6.10	13.1	10.2	3.48	1.13	0.266	0.056	0.156	0.499
LT/SN/Km2	7.48	21.0	27.8	18.4	39.4	30.8	10.5	3.39	0.801	0.169	0.469	1.50
AKIM mm.	20.0	54.4	74.5	49.2	95.2	82.4	27.2	9.09	2.08	0.453	1.26	3.89
MİL. M3	6.65	18.1	24.7	16.3	31.6	27.4	9.03	3.02	0.689	0.151	0.417	1.29

SU YILI (2006) YILLIK TOPLAM AKIM 139.35 MİLYON M3 420 MM. 13.3 LT/SN/Km2

13. Bati Karadeniz Havzasi

D13A040 GEREDE ÇAYI BAHÇEDERE

YERİ : **GEREDE-KARABÜK YOLUNUN 10.KM SİNDEN SAĞA AYRILAN YOLUN 5.KM SİNDE İMAMLAR (BAHÇEDERE) KÖYÜNDEDIR.**
32°19'0" Doğu - 40°48'0" Kuzey

YAĞIŞ ALANI : **1343.00 km2** **YAKLAŞIK KOT : 1095 m**

GÖZLEM SÜRESİ : **01.10.1974 - 30.09.2006**

ORTALAMA AKIMLAR : **Gözlem süresinde 8.262 m3/sn. (29 Yıllık) 2006 Su yılında 6.895 m3/sn.**

ANLIK EN ÇOK VE EN AZ AKIMLAR:

2006 Su yılında anlık ençok akım	**:**	**52.3**	**m3/sn**	**25.03.2006**
2006 Su yılında anlık enaz akım	**:**	**0.062**	**m3/sn**	**07.08.2006**
Gözlem süresinde anlık ençok akım	**:**	**216.**	**m3/sn**	**27.02.1989**
Gözlem süresinde anlık enaz akım	**:**	**0.050**	**m3/sn**	**24.08.1988**

8. Anahtar Eğrisi (Seviyeler cm olarak)

Seviye	Akım	Seviye	Akım	Seviye	Akım	Seviye	Akım
59	0.377	110	10.0	210	63.2	300	142.
62	0.659	130	17.0	230	79.5	320	160.
66	1.1	150	26.4	250	97.0	340	180.
70	1.5	170	37.5	260	106.	360	200.
90	4.9	190	49.3	280	124.	380	220.

Akımlar 01 Ekim 2005 'den 30 Eylül 2006' a kadar m3/sn olarak

Gün	Ekim	Kasım	Aralık	Ocak	Şubat	Mart	Nisan	Mayıs	Haziran	Temmuz	Ağustos	Eylül
01	0.440	0.770	5.93	4.00	1.86	39.4	38.2	10.4	2.23	0.560	0.180	0.135
02	0.440	0.770	4.80	3.83	1.74	37.6	34.6	14.3	2.11	0.560	0.135	0.180
03	0.500	0.770	4.35	3.48	1.74	34.0	31.0	13.9	1.99	0.560	0.135	0.273
04	0.630	0.700	4.35	3.13	1.62	31.6	28.2	11.9	1.74	0.630	0.135	0.320
05	0.700	0.700	4.18	2.95	1.62	27.0	25.9	10.1	1.49	0.630	0.135	0.273
06	0.630	0.840	4.00	3.30	1.62	27.0	25.3	9.21	1.37	0.700	0.135	0.273
07	0.560	0.910	3.65	3.48	1.74	28.2	25.9	8.92	1.28	0.630	0.099	0.273
08	0.560	1.00	2.60	3.65	1.74	29.9	30.4	9.50	1.28	0.500	0.062	0.273
09	0.560	1.09	2.35	3.65	1.74	29.9	37.0	8.63	1.28	0.500	0.062	0.225
10	0.500	1.09	2.11	3.65	1.86	23.2	36.4	8.05	1.37	0.440	0.062	0.225
11	0.560	1.00	1.86	3.13	1.86	22.7	36.4	6.89	1.28	0.380	0.062	0.225
12	0.630	1.00	1.74	2.35	1.86	27.0	37.0	6.38	1.37	0.320	0.062	0.273
13	0.630	0.910	1.62	2.23	1.99	33.4	43.0	6.89	1.62	0.320	0.062	0.273
14	0.630	1.00	1.49	2.11	2.23	43.0	42.4	6.89	1.37	0.273	0.062	0.273
15	0.700	1.19	1.37	1.99	2.23	43.0	38.2	6.15	1.37	0.273	0.062	0.273
16	0.700	1.19	1.49	1.99	2.35	29.9	34.0	5.70	1.28	0.273	0.062	0.273
17	0.630	1.19	1.62	1.86	2.35	24.2	28.7	5.70	1.09	0.225	0.062	0.273
18	0.700	1.09	1.62	1.86	2.35	21.1	24.8	5.70	1.00	0.180	0.062	0.273
19	0.700	1.28	1.99	1.74	3.30	17.2	21.6	5.48	0.840	0.225	0.062	0.225
20	0.910	2.35	3.65	1.99	6.38	16.4	21.1	5.03	0.840	0.225	0.062	0.180
21	1.09	5.03	3.30	1.62	10.7	15.7	21.1	4.58	0.700	0.180	0.062	0.225
22	1.00	4.80	3.83	1.62	14.3	16.4	18.8	4.58	0.560	0.225	0.062	0.225
23	0.840	3.65	4.58	1.49	16.4	27.0	16.8	4.35	0.560	0.225	0.062	0.320
24	0.770	3.83	4.58	1.62	20.0	46.9	16.0	4.35	0.630	0.225	0.062	0.440
25	0.770	3.13	4.58	1.62	21.1	47.6	13.9	4.18	0.560	0.180	0.062	0.700
26	0.770	3.48	4.58	1.86	35.2	39.4	11.6	4.00	0.500	0.225	0.062	0.700
27	0.770	8.34	4.00	1.99	45.6	35.2	9.50	3.83	0.440	0.273	0.062	0.560
28	0.840	11.9	3.30	1.86	43.0	32.2	8.05	3.48	0.380	0.273	0.062	0.500
29	0.840	9.21	2.78	1.74	-----	32.2	7.76	2.95	0.440	0.225	0.099	0.500
30	0.840	7.76	3.30	1.74	-----	33.4	8.92	2.60	0.560	0.225	0.099	0.500
31	0.770	-----	3.83	1.86	-----	40.0	-----	2.35	-----	0.180	0.099	-----
Maks.	1.09	13.2	6.15	4.00	48.2	52.3	43.7	15.0	2.23	0.770	0.180	0.770
Min.	0.440	0.700	1.28	1.49	1.62	15.0	7.47	2.35	0.380	0.180	0.062	0.135
Ortalama	0.697	2.73	3.21	2.43	8.95	30.7	25.8	6.68	1.12	0.350	0.082	0.322
LT/SN/Km2	0.519	2.03	2.39	1.81	6.66	22.9	19.2	4.97	0.832	0.260	0.061	0.240
AKIM mm.	1.39	5.27	6.40	4.85	16.1	61.2	49.7	13.3	2.16	0.697	0.164	0.622
MİL. M3	1.87	7.08	8.59	6.51	21.6	82.2	66.7	17.9	2.90	0.937	0.221	0.835

SU YILI (2006) YILLIK TOPLAM AKIM 217.34 MİLYON M3 162 MM. 5.1 LT/SN/Km2

13. Bati Karadeniz Havzasi

D13A041 FİLYOS Ç. BALIKISIK

YERİ : KARABÜK'TEN YENİCE KARAYOLU İSTİKAMETİNE GİDİLDİĞİNDE YENİCE'YE 5 KM. MESAFEDE BALIKISIK'TADIR

32°24'0" Doğu - 41°12'0" Kuzey

YAĞIŞ ALANI : 8310,00 km2 YAKLAŞIK KOT : 140 m

GÖZLEM SÜRESİ : 01.10.1978 - 30.09.2006

ORTALAMA AKIMLAR : Gözlem süresinde 47.501 m3/sn. (21 Yıllık) 2006 Su yılında 26.772 m3/sn.

ANLIK EN ÇOK VE EN AZ AKIMLAR:

2006 Su yılında anlık ençok akım	:	272.	m3/sn	04.03.2006
2006 Su yılında anlık enaz akım	:	2.36	m3/sn	05.09.2006
Gözlem süresinde anlık ençok akım	:	1215	m3/sn	07.07.1991
Gözlem süresinde anlık enaz akım	:	0.131	m3/sn	19.12.2001

2011. Anahtar Eğrisi (Seviyeler cm olarak)

Seviye	Akım	Seviye	Akım	Seviye	Akım	Seviye	Akım
30	0.007	94	10.1	160	82.0	268	330.
42	0.095	107	17.9	174	108.	303	426.
55	0.606	120	29.0	192	144.	348	556.
68	2.0	133	43.1	213	190.	404	715.
81	4.9	147	61.3	238	252.	474	916.

Akımlar 01 Ekim 2005 'den 30 Eylül 2006' a kadar m3/sn olarak

Gün	Ekim	Kasım	Aralık	Ocak	Şubat	Mart	Nisan	Mayıs	Haziran	Temmuz	Ağustos	Eylül
01	5.16	7.47	33.8	14.4	13.0	176.	79.1	46.4	12.2	11.5	2.47	2.58
02	5.16	7.47	27.6	14.4	13.0	178.	79.1	48.2	10.8	10.2	2.58	2.58
03	5.16	7.47	25.6	14.4	13.0	183.	79.1	49.9	10.2	9.69	2.58	2.58
04	5.16	7.47	24.1	21.1	13.0	200.	79.1	51.7	10.2	10.2	2.58	2.47
05	5.16	7.47	24.1	26.4	13.0	159.	79.1	51.7	9.69	9.69	2.58	2.36
06	5.16	7.47	24.1	31.3	13.0	123.	81.8	49.9	8.58	8.58	2.58	2.36
07	5.16	7.47	22.6	39.9	14.4	116.	84.5	48.2	8.58	8.02	2.58	2.47
08	5.16	7.47	21.1	49.9	15.8	121.	84.5	53.5	8.02	7.47	2.90	2.47
09	5.16	7.47	19.5	41.1	15.8	138.	84.5	55.3	8.02	6.36	2.90	2.47
10	5.16	7.47	18.0	35.0	15.8	123.	84.5	57.0	8.02	5.48	2.90	2.47
11	5.16	7.47	17.3	31.3	15.8	109.	84.5	55.3	8.02	5.48	3.22	2.47
12	5.16	7.47	16.6	26.4	15.8	105.	84.5	51.7	8.02	5.48	2.90	2.58
13	5.16	7.47	15.8	24.9	15.8	95.6	84.5	49.9	8.02	5.16	2.90	2.90
14	5.16	7.47	15.1	23.3	15.8	95.6	84.5	51.7	8.02	5.16	2.90	2.90
15	5.16	7.47	15.1	21.8	15.8	123.	84.5	38.7	8.02	4.83	3.22	2.90
16	5.16	7.47	15.1	21.1	15.8	145.	84.5	37.4	8.02	4.19	2.90	2.90
17	5.16	7.47	15.1	18.8	15.8	119.	84.5	32.5	8.02	4.51	3.22	2.90
18	5.16	7.47	15.1	17.3	15.8	105.	79.1	31.3	8.02	4.19	3.55	2.90
19	6.36	7.47	15.1	18.8	15.8	95.6	75.0	28.9	8.02	3.87	3.22	2.90
20	7.47	7.47	15.1	18.8	15.8	88.6	72.3	24.1	8.02	3.87	3.22	2.90
21	7.47	7.47	15.1	18.0	15.8	84.5	72.3	22.6	8.02	3.87	3.22	2.90
22	7.47	7.47	15.1	17.3	15.8	80.4	69.5	23.3	8.02	3.87	2.90	2.90
23	7.47	7.47	15.1	17.3	15.8	79.1	68.2	20.3	8.02	3.55	2.90	3.22
24	7.47	7.47	15.1	16.6	15.8	79.1	66.8	19.5	8.02	3.22	2.90	3.22
25	7.47	7.47	15.1	15.8	15.8	79.1	62.3	18.8	7.47	3.22	2.90	3.22
26	7.47	7.47	14.4	15.8	15.8	79.1	58.8	17.3	6.91	3.55	2.90	3.22
27	7.47	7.47	14.4	15.1	81.8	79.1	55.3	17.3	6.91	3.22	2.90	3.22
28	7.47	7.47	14.4	15.1	178.	79.1	51.7	17.3	6.91	3.22	2.58	3.22
29	7.47	21.1	14.4	14.4	-----	79.1	49.9	17.3	6.91	2.58	2.90	3.22
30	7.47	42.9	14.4	13.0	-----	79.1	46.4	15.1	6.91	2.58	2.90	3.22
31	7.47	-----	14.4	13.0	-----	79.1	-----	13.7	-----	2.58	2.90	-----
Maks.	7.47	44.6	37.4	53.5	215.	272.	87.2	57.0	13.0	11.5	6.91	3.22
Min.	5.16	7.47	14.4	12.2	12.2	79.1	46.4	13.7	6.36	2.47	2.47	2.36
Ortalama	6.09	9.11	18.0	22.0	23.3	112.	74.5	36.0	8.29	5.46	2.90	2.82
LT/SN/Km2	0.733	1.10	2.17	2.65	2.80	13.5	8.96	4.33	0.997	0.658	0.349	0.339
AKIM mm.	1.96	2.84	5.80	7.09	6.78	36.1	23.2	11.6	2.58	1.76	0.934	0.880
MİL. M3	16.3	23.6	48.2	58.9	56.4	300.	193.	96.4	21.5	14.6	7.76	7.31

SU YILI (2006) YILLIK TOPLAM AKIM 843.97 MİLYON M3 102 MM. 3.2 LT/SN/Km2

13. Bati Karadeniz Havzasi

D13A042 İHSANİYE D. İHSANİYE

YERİ : ZONGULDAK'IN MERKEZ KOZLU BELDESİ İÇINDEKI İHSANIYE CAMISININ YANINDADIR.
31°46'21" Doğu - 41°25'24" Kuzey

YAĞIŞ ALANI : 10,15 km2 YAKLAŞIK KOT : 15 m

GÖZLEM SÜRESİ : 01.09.1981 - 30.09.2006

ORTALAMA AKIMLAR : Gözlem süresinde 0.432 m3/sn. (20 Yıllık) 2006 Su yılında 0.371 m3/sn.

ANLIK EN ÇOK VE EN AZ AKIMLAR:

2006 Su yılında anlık ençok akım	:	23.5	m3/sn	20.11.2005
2006 Su yılında anlık enaz akım	:	0.008	m3/sn	21.09.2006
Gözlem süresinde anlık ençok akım	:	42.4	m3/sn	07.07.1991
Gözlem süresinde anlık enaz akım	:	0.000	m3/sn	17.10.1984

6. Anahtar Eğrisi (Seviyeler cm olarak)

Seviye	Akım	Seviye	Akım	Seviye	Akım	Seviye	Akım
40	0.002	85	3.9	120	13.5	169	0.000
50	0.014	90	5.0	130	17.0	170	32.0
55	0.040	95	6.3	140	20.0	180	36.0
65	0.520	100	7.6	150	24.0	190	40.0
75	1.9	110	10.5	160	28.0	200	44.0

Akımlar 01 Ekim 2005 'den 30 Eylül 2006' a kadar m3/sn olarak

Gün	Ekim	Kasım	Aralık	Ocak	Şubat	Mart	Nisan	Mayıs	Haziran	Temmuz	Ağustos	Eylül
01	0.086	2.10	0.180	0.800	0.540	0.933	0.180	0.108	0.086	0.086	0.039	0.050
02	0.086	1.20	0.180	0.540	0.640	0.933	0.180	0.108	0.086	0.086	0.039	0.068
03	0.086	0.933	0.180	0.540	0.540	1.56	0.180	0.108	0.068	0.086	0.039	0.068
04	0.068	0.800	0.130	0.440	0.540	1.07	0.180	0.108	0.068	0.086	0.039	0.086
05	0.068	0.720	0.285	0.440	0.440	0.720	0.180	0.108	0.068	0.086	0.039	0.086
06	0.050	0.540	0.230	0.230	0.540	0.640	0.180	0.108	0.068	0.086	0.039	0.086
07	0.050	0.540	0.180	0.640	0.640	0.640	0.180	0.108	0.050	0.086	0.039	0.086
08	0.050	0.933	0.180	1.07	0.640	0.640	0.180	0.108	0.068	0.086	0.039	0.086
09	0.050	0.800	0.180	0.640	0.540	0.640	0.130	0.130	0.086	0.086	0.027	0.086
10	0.050	0.640	0.180	0.540	0.720	0.540	0.130	0.068	0.130	0.086	0.027	0.086
11	0.050	0.540	0.180	0.390	0.933	0.540	0.130	0.108	0.130	0.068	0.019	0.086
12	0.050	0.390	0.180	0.108	1.07	0.390	0.108	0.108	0.130	0.068	0.019	0.086
13	0.050	0.390	0.130	0.340	0.800	0.340	0.108	0.180	0.130	0.068	0.019	0.086
14	0.068	0.540	0.180	0.800	0.640	0.340	0.108	0.130	0.800	0.068	0.019	0.086
15	0.390	1.92	0.180	0.640	0.640	0.285	0.108	0.108	0.340	0.068	0.019	0.086
16	0.440	1.20	0.285	0.440	0.540	0.285	0.108	0.108	0.180	0.068	0.027	0.086
17	2.10	0.933	0.440	0.440	0.800	0.285	0.108	0.108	0.108	0.068	0.050	0.086
18	0.640	0.640	0.230	0.130	1.38	0.230	0.108	0.086	0.086	0.068	0.039	0.086
19	1.92	0.440	1.38	0.130	1.07	0.230	0.086	0.086	0.086	0.050	0.039	0.068
20	4.65	4.65	0.933	0.933	0.933	0.230	0.086	0.086	0.086	0.068	0.027	0.068
21	1.56	7.62	0.640	0.540	0.800	0.230	0.108	0.086	0.086	0.050	0.027	0.050
22	0.933	1.92	0.540	0.540	0.720	0.230	0.108	0.086	0.086	0.050	0.027	0.068
23	0.800	0.800	0.540	0.540	0.640	0.230	0.108	0.086	0.086	0.050	0.027	0.068
24	0.640	0.440	0.540	0.540	0.640	0.230	0.108	0.086	0.086	0.050	0.027	0.068
25	0.540	0.390	0.440	0.440	0.640	0.230	0.108	0.086	0.086	0.050	0.027	0.086
26	0.440	0.285	0.640	0.440	0.640	0.230	0.108	0.086	0.086	0.050	0.027	0.108
27	0.390	0.230	0.933	0.390	0.640	0.230	0.108	0.086	0.086	0.050	0.027	0.086
28	0.390	0.180	2.10	0.285	0.720	0.230	0.108	0.086	0.086	0.050	0.027	0.108
29	0.390	0.180	1.38	0.180	-----	0.230	0.108	0.086	0.086	0.050	0.039	0.108
30	1.74	0.180	1.07	0.340	-----	0.230	0.108	0.086	0.086	0.050	0.039	0.933
31	1.92	-----	1.07	0.340	-----	0.230	-----	0.086	-----	0.050	0.039	-----
Maks.	8.40	23.5	2.79	2.56	1.56	1.74	0.180	0.180	1.38	0.086	0.068	4.09
Min.	0.039	0.180	0.108	0.027	0.440	0.180	0.086	0.068	0.050	0.050	0.019	0.008
Ortalama	0.669	1.10	0.513	0.478	0.715	0.452	0.128	0.101	0.124	0.067	0.031	0.110
LT/SN/Km2	65.9	109.	50.6	47.1	70.5	44.5	12.6	9.90	12.2	6.59	3.10	10.8
AKIM mm.	177.	282.	135.	126.	170.	119.	32.7	26.5	31.6	17.6	8.31	28.0
MİL. M3	1.79	2.86	1.38	1.28	1.73	1.21	0.332	0.269	0.321	0.179	0.084	0.285

SU YILI (2006) YILLIK TOPLAM AKIM 11.72 MİLYON M3 1155 MM. 36.6 LT/SN/Km2

13. Bati Karadeniz Havzasi

D13A044 BOLU Ç. DEVREK

YERİ : **DEVREK-BOLU KARAYOLUNUN 4.KM SİNDEDIR.**
31°56'20" Doğu - 41°11'29" Kuzey

YAĞIŞ ALANI : **2917,40 km2** **YAKLAŞIK KOT : 100 m**

GÖZLEM SÜRESİ : **06.01.1982 - 30.09.2006**

ORTALAMA AKIMLAR : **Gözlem süresinde 23.458 m3/sn. (21 Yıllık) 2006 Su yılında 18.352 m3/sn.**

ANLIK EN ÇOK VE EN AZ AKIMLAR:

2006 Su yılında anlık ençok akım	**:**	**108.**	**m3/sn**	**04.03.2006**
2006 Su yılında anlık enaz akım	**:**	**2.82**	**m3/sn**	**25.08.2006**
Gözlem süresinde anlık ençok akım	**:**	**460.**	**m3/sn**	**07.07.1991**
Gözlem süresinde anlık enaz akım	**:**	**1.21**	**m3/sn**	**16.02.2001**

Akımlar 01 Ekim 2005 'den 30 Eylül 2006' a kadar m3/sn olarak

Gün	Ekim	Kasım	Aralık	Ocak	Şubat	Mart	Nisan	Mayıs	Haziran	Temmuz	Ağustos	Eylül
01	3.64	9.20	24.2	42.0	17.3	68.8	31.8	16.3	8.50	6.50	4.00	3.60
02	3.80	8.25	19.2	34.8	17.0	69.7	31.8	16.7	7.75	6.00	4.00	5.40
03	3.96	7.75	18.0	31.3	17.3	84.9	31.3	17.0	7.25	5.80	4.00	5.20
04	4.12	7.00	17.3	28.0	20.6	97.4	29.6	16.3	7.25	7.75	4.00	4.60
05	3.80	7.50	21.5	25.8	21.5	73.9	28.0	16.0	7.00	7.75	4.00	4.20
06	3.80	8.25	19.2	26.6	22.5	60.8	27.4	16.3	6.75	6.75	3.80	4.00
07	3.80	10.6	17.3	32.9	22.9	57.2	27.0	16.3	6.75	6.00	3.80	3.80
08	3.64	12.7	16.3	38.6	22.0	57.2	26.6	16.3	7.00	5.80	3.80	3.60
09	3.64	11.7	15.3	35.8	21.5	61.5	25.4	16.3	8.50	5.60	3.80	3.60
10	3.48	10.6	14.0	30.7	23.4	54.3	27.0	18.4	8.50	5.40	3.60	3.40
11	3.31	9.20	12.7	26.2	55.0	52.9	27.4	18.0	8.85	5.20	3.60	3.40
12	3.80	8.25	12.3	24.6	50.0	58.6	27.0	17.3	10.3	5.20	3.60	3.80
13	5.40	7.75	12.0	22.9	38.2	66.6	27.0	18.7	10.3	5.00	3.60	3.80
14	5.40	8.25	12.0	21.1	33.4	63.0	26.6	21.5	11.7	5.00	3.60	3.60
15	5.60	8.50	12.0	19.2	28.5	57.2	26.2	18.7	10.6	4.80	3.60	3.80
16	5.60	8.25	12.0	18.0	24.2	50.7	25.4	17.3	8.85	4.80	3.40	3.80
17	5.80	8.50	13.7	17.0	22.0	46.4	23.8	15.3	8.25	4.80	3.40	3.80
18	5.80	8.85	13.0	17.0	28.0	40.6	22.0	14.6	8.00	4.60	3.40	3.80
19	7.25	8.50	13.7	18.0	57.2	39.1	21.1	14.6	8.00	4.40	3.40	4.00
20	27.4	9.55	16.3	20.6	75.6	37.7	21.1	14.3	7.75	4.20	3.20	4.00
21	21.5	17.3	14.6	18.7	85.8	36.3	20.6	13.7	7.25	4.20	3.20	4.60
22	15.6	18.4	13.3	18.7	82.4	35.8	20.1	13.0	7.00	4.20	3.00	4.80
23	12.0	16.7	12.7	20.6	74.8	35.8	18.7	11.7	6.50	4.20	3.00	4.80
24	11.0	36.3	13.3	20.1	69.7	40.1	17.7	11.0	6.25	4.20	3.00	5.20
25	9.90	60.8	14.3	18.7	66.6	44.2	17.3	10.3	6.00	4.20	2.82	7.00
26	9.55	62.2	15.0	18.4	84.1	39.6	17.0	9.90	5.80	4.20	2.82	5.20
27	8.85	48.5	16.0	18.0	90.0	37.2	17.0	9.90	5.60	4.00	2.82	4.60
28	8.25	41.0	26.6	17.7	75.6	35.3	16.7	9.55	6.25	4.00	2.82	4.40
29	8.00	33.4	35.3	16.7	-----	34.3	16.3	9.55	7.00	4.00	2.82	4.40
30	8.25	28.5	36.7	16.0	-----	33.9	16.3	9.20	7.50	4.00	2.82	7.25
31	8.50	-----	39.1	16.0	-----	32.9	-----	9.20	-----	4.00	3.00	-----
Maks.	32.4	67.3	44.2	42.7	92.5	108.	31.8	22.5	11.7	10.3	4.00	8.85
Min.	3.31	7.00	11.7	15.6	16.7	32.9	16.3	9.20	5.60	4.00	2.82	3.20
Ortalama	7.56	18.1	17.7	23.6	44.5	51.7	23.7	14.6	7.77	5.05	3.41	4.38
LT/SN/Km2	2.59	6.20	6.07	8.08	15.3	17.7	8.13	5.01	2.66	1.73	1.17	1.50
AKIM mm.	6.94	16.1	16.3	21.6	36.9	47.5	21.1	13.4	6.90	4.64	3.13	3.89
MİL. M3	20.3	46.9	47.4	63.1	108.	139.	61.4	39.2	20.1	13.5	9.13	11.4

SU YILI (2006) YILLIK TOPLAM AKIM 579.43 MİLYON M3 199 MM. 6.3 LT/SN/Km2

13. Bati Karadeniz Havzasi

D13A045 ULUSU DERESİ YAĞBAŞLAR

YERİ : GEREDE' DEN DÖRTDİVAN'A GİDİLİR. DÖRTDİVAN KARTALKAYA YOLUNUN 10.KM SİNDEKİ YAĞBAŞLAR KÖYÜNÜN İÇİNDEDİR.
31°59'0" Doğu - 40°41'0" Kuzey

YAĞIŞ ALANI : 196.00 km2 YAKLAŞIK KOT : 1183 m

GÖZLEM SÜRESİ : 01.02.1982 - 30.09.2006

ORTALAMA AKIMLAR : Gözlem süresinde 2.000 m3/sn. (23 Yıllık) 2006 Su yılında 1.476 m3/sn.

ANLIK EN ÇOK VE EN AZ AKIMLAR:

2006 Su yılında anlık ençok akım	:	10.7	m3/sn	24.03.2006
2006 Su yılında anlık enaz akım	:	0.064	m3/sn	06.08.2006
Gözlem süresinde anlık ençok akım	:	55.1	m3/sn	21.05.1998
Gözlem süresinde anlık enaz akım	:	0.000	m3/sn	24.10.1992

8. Anahtar Eğrisi (Seviyeler cm olarak)

Seviye	Akım	Seviye	Akım	Seviye	Akım	Seviye	Akım
4	0.025	10	0.450	35	5.6	70	18.0
6	0.118	15	1.1	40	7.0	80	22.0
7	0.180	20	2.0	45	8.6	90	26.5
8	0.270	25	3.0	50	10.3	100	31.5
9	0.350	30	4.2	60	14.0	110	36.5

Akımlar 01 Ekim 2005 'den 30 Eylül 2006' a kadar m3/sn olarak

Gün	Ekim	Kasım	Aralık	Ocak	Şubat	Mart	Nisan	Mayıs	Haziran	Temmuz	Ağustos	Eylül
01	0.118	0.270	1.44	0.970	0.450	4.20	6.42	3.24	0.970	0.270	0.118	0.118
02	0.118	0.270	1.44	0.840	0.450	5.01	5.84	3.24	0.840	0.270	0.118	0.118
03	0.180	0.270	1.44	0.840	0.450	6.71	5.55	3.00	0.840	0.270	0.118	0.118
04	0.180	0.270	1.44	0.710	0.450	5.01	5.28	2.79	0.840	0.350	0.118	0.118
05	0.180	0.270	1.27	0.840	0.450	3.72	5.01	2.58	0.710	0.270	0.118	0.118
06	0.180	0.270	1.10	0.840	0.450	3.72	5.01	2.37	0.580	0.270	0.064	0.118
07	0.118	0.270	0.970	0.970	0.450	4.20	5.01	2.37	0.580	0.180	0.064	0.118
08	0.118	0.350	0.970	0.970	0.450	5.55	7.00	2.37	0.580	0.180	0.064	0.118
09	0.118	0.350	0.840	0.970	0.450	5.01	7.66	2.37	0.580	0.180	0.064	0.118
10	0.118	0.350	0.710	1.10	0.450	4.47	7.33	1.95	0.580	0.180	0.064	0.118
11	0.118	0.350	0.710	1.27	0.450	3.72	7.66	1.95	0.840	0.118	0.064	0.118
12	0.180	0.350	0.450	0.840	0.450	4.20	7.99	1.95	0.840	0.118	0.064	0.118
13	0.180	0.350	0.450	0.840	0.450	5.55	9.64	2.37	0.580	0.118	0.064	0.118
14	0.180	0.350	0.450	0.710	0.450	5.28	8.65	2.16	0.580	0.118	0.064	0.118
15	0.180	0.350	0.350	0.710	0.450	5.01	7.99	1.95	0.450	0.118	0.064	0.118
16	0.180	0.350	0.350	0.580	0.450	4.20	7.33	1.95	0.450	0.118	0.064	0.118
17	0.180	0.350	0.350	0.450	0.450	3.72	6.42	2.16	0.450	0.118	0.064	0.118
18	0.180	1.10	0.450	0.450	0.970	3.24	6.13	1.95	0.450	0.118	0.064	0.118
19	0.180	1.61	1.27	0.450	1.27	2.79	5.55	1.95	0.350	0.118	0.064	0.180
20	0.270	1.61	1.10	0.450	2.16	2.58	5.55	1.95	0.270	0.118	0.064	0.350
21	0.270	1.10	1.10	0.450	2.37	2.79	5.55	1.95	0.270	0.118	0.064	0.350
22	0.270	0.710	1.10	0.450	2.58	3.96	5.01	1.95	0.270	0.118	0.064	0.270
23	0.270	0.710	1.10	0.450	2.79	6.13	4.47	1.78	0.270	0.118	0.064	0.118
24	0.270	0.840	0.970	0.450	3.24	9.64	4.20	1.78	0.270	0.118	0.064	0.118
25	0.270	1.61	0.840	0.450	3.48	8.98	3.72	1.78	0.270	0.118	0.064	0.118
26	0.270	2.58	0.970	0.450	4.74	9.31	3.00	1.61	0.270	0.118	0.064	0.118
27	0.270	2.79	1.10	0.450	4.74	6.42	2.79	1.61	0.180	0.118	0.064	0.118
28	0.270	2.16	0.970	0.450	3.72	5.28	2.37	1.44	0.270	0.118	0.064	0.118
29	0.270	1.78	0.970	0.450	-----	5.55	2.37	1.27	0.270	0.118	0.064	0.118
30	0.270	1.44	0.970	0.450	-----	5.84	2.58	1.10	0.270	0.118	0.064	0.180
31	0.270	-----	0.970	0.450	-----	7.00	-----	0.970	-----	0.118	0.064	-----
Maks.	0.270	2.79	1.44	1.44	5.28	10.7	10.3	3.24	0.970	0.450	0.118	0.350
Min.	0.118	0.270	0.350	0.450	0.450	2.16	2.37	0.970	0.180	0.118	0.064	0.118
Ortalama	0.201	0.848	0.923	0.669	1.42	5.12	5.64	2.06	0.499	0.158	0.073	0.143
LT/SN/Km2	1.02	4.32	4.71	3.42	7.24	26.1	28.8	10.5	2.55	0.806	0.371	0.728
AKIM mm.	2.74	11.2	12.6	9.15	17.5	70.0	74.5	28.2	6.60	2.16	0.994	1.89
MİL. M3	0.538	2.20	2.47	1.79	3.43	13.7	14.6	5.52	1.29	0.423	0.195	0.370

SU YILI (2006) YILLIK TOPLAM AKIM 46.53 MİLYON M3 237 MM. 7.5 LT/SN/Km2

13. Bati Karadeniz Havzasi

D13A046 MARKOŞA D. SALUR KÖPRÜSÜ

YERİ : **GEREDE SALUR YOLUNDA SALUR KÖYÜ 100 M. MANSABINDADIR**
32°59'27" Doğu - 40°45'43" Kuzey

YAĞIŞ ALANI : **240.00 km2** **YAKLAŞIK KOT : 1200 m**

GÖZLEM SÜRESİ : **01.02.1982 - 30.09.2006**

ORTALAMA AKIMLAR : **Gözlem süresinde 2.126 m3/sn. (20 Yıllık) 2006 Su yılında 1.942 m3/sn.**

ANLIK EN ÇOK VE EN AZ AKIMLAR:

2006 Su yılında anlık ençok akım	**:**	**23.3**	**m3/sn**	**24.03.2006**
2006 Su yılında anlık enaz akım	**:**	**0.009**	**m3/sn**	**04.08.2006**
Gözlem süresinde anlık ençok akım	**:**	**80.0**	**m3/sn**	**30.01.1987**
Gözlem süresinde anlık enaz akım	**:**	**0.000**	**m3/sn**	**29.06.1986**

İstasyon için kullanılmış anahtar bulunamadı.

Akımlar 01 Ekim 2005 'den 30 Eylül 2006' a kadar m3/sn olarak

Gün	Ekim	Kasım	Aralık	Ocak	Şubat	Mart	Nisan	Mayıs	Haziran	Temmuz	Ağustos	Eylül
01	0.137	0.310	1.62	1.48	1.12	5.52	12.2	3.62	0.610	0.230	0.056	0.137
02	0.137	0.310	1.35	1.12	1.12	5.20	10.6	3.62	0.535	0.310	0.056	0.230
03	0.230	0.310	1.22	0.930	1.12	6.16	9.24	5.84	0.535	0.460	0.056	0.137
04	0.310	0.310	1.22	0.930	1.12	8.00	8.40	4.93	0.460	0.460	0.009	0.137
05	0.230	0.385	1.02	0.930	1.12	5.52	7.20	3.85	0.460	0.385	0.009	0.137
06	0.137	0.385	0.930	1.35	1.12	5.84	7.20	3.16	0.385	0.310	0.009	0.137
07	0.137	0.385	0.770	1.48	1.12	6.80	7.60	2.70	0.385	0.230	0.009	0.056
08	0.137	0.385	0.690	1.35	1.12	8.00	10.6	2.54	0.385	0.230	0.009	0.056
09	0.137	0.385	0.690	1.12	1.12	7.20	13.3	2.54	0.385	0.230	0.009	0.056
10	0.137	0.385	0.610	1.12	1.12	5.84	12.2	2.37	0.460	0.230	0.009	0.056
11	0.137	0.310	0.535	1.12	1.12	4.12	11.6	2.04	0.385	0.230	0.009	0.056
12	0.230	0.310	0.535	1.12	1.12	5.20	12.7	1.88	0.460	0.230	0.009	0.056
13	0.230	0.310	0.460	1.12	1.12	8.40	17.0	1.75	0.385	0.137	0.009	0.056
14	0.230	0.385	0.460	1.12	1.12	12.2	13.9	1.75	0.385	0.137	0.009	0.056
15	0.230	0.535	0.385	1.12	1.12	9.68	11.0	1.62	0.385	0.056	0.009	0.056
16	0.230	0.460	0.460	1.12	1.12	6.48	9.24	1.48	0.385	0.056	0.009	0.056
17	0.230	0.385	0.460	1.12	1.12	4.93	7.20	1.48	0.310	0.056	0.009	0.056
18	0.230	0.385	0.460	1.12	1.12	3.62	6.48	1.48	0.310	0.056	0.056	0.056
19	0.230	0.690	0.930	1.12	1.12	3.16	5.52	1.35	0.230	0.056	0.056	0.056
20	0.310	1.22	1.22	1.12	1.12	2.37	5.52	1.35	0.230	0.056	0.056	0.056
21	0.310	1.75	1.22	1.12	1.62	2.54	5.84	1.22	0.230	0.056	0.056	0.056
22	0.310	1.12	1.22	1.12	2.37	3.16	5.20	1.22	0.137	0.056	0.056	0.056
23	0.230	1.12	1.22	1.12	3.16	8.80	4.66	1.12	0.137	0.056	0.056	0.137
24	0.230	0.930	1.22	1.12	3.39	18.8	4.66	1.12	0.137	0.310	0.056	0.230
25	0.230	1.22	1.22	1.12	3.85	16.3	3.85	1.02	0.137	0.310	0.056	0.310
26	0.230	2.37	1.22	1.12	6.16	10.6	2.93	1.02	0.137	0.230	0.056	0.230
27	0.230	3.62	1.22	1.12	6.80	9.24	2.37	0.930	0.137	0.230	0.056	0.230
28	0.230	3.62	1.22	1.12	5.20	8.00	2.04	0.850	0.137	0.230	0.056	0.137
29	0.310	2.54	1.12	1.12	-----	8.80	2.04	0.770	0.137	0.137	0.056	0.137
30	0.310	2.21	1.02	1.12	-----	10.6	2.70	0.690	0.230	0.137	0.137	0.230
31	0.310	-----	1.12	1.12	-----	15.1	-----	0.610	-----	0.137	0.137	-----
Maks.	0.310	5.52	1.88	1.75	8.80	23.3	19.4	6.48	0.610	1.48	0.137	0.535
Min.	0.137	0.230	0.310	0.850	1.12	2.04	1.88	0.610	0.137	0.056	0.009	0.056
Ortalama	0.224	0.968	0.937	1.14	1.96	7.62	7.83	2.00	0.321	0.195	0.040	0.115
LT/SN/Km2	0.934	4.03	3.90	4.75	8.18	31.7	32.6	8.32	1.34	0.811	0.167	0.479
AKIM mm.	2.50	10.5	10.5	12.7	19.8	85.0	84.6	22.3	3.46	2.17	0.446	1.24
MİL. M3	0.600	2.51	2.51	3.05	4.75	20.4	20.3	5.35	0.831	0.521	0.107	0.298

SU YILI (2006) YILLIK TOPLAM AKIM 61.23 MİLYON M3 255 MM. 8.1 LT/SN/Km2

13. Bati Karadeniz Havzasi

D13A047 DEREKÖY D. YÜZBAŞIPINARI

YERİ : **ESKİ ZONGULDAK-ANKARA KARAYOLUNUN 18.KM.SINDEN KUMTARLA KÖYÜ İSTIKAMETINE DÖNÜLEREK TAŞÇILAR KÖYÜNE VARILIR. AGİ KÖYÜN MERKEZINDEDIR. 31°51'0" Doğu - 41°20'25" Kuzey**

YAĞIŞ ALANI : **41,80 km2** **YAKLAŞIK KOT : 350 m**

GÖZLEM SÜRESİ : **14.10.1982 - 30.09.2006**

ORTALAMA AKIMLAR : **Gözlem süresinde 0.923 m3/sn. (12 Yıllık) 2006 Su yılında 0.748 m3/sn.**

ANLIK EN ÇOK VE EN AZ AKIMLAR:

2006 Su yılında anlık ençok akım	**:**	**11.5**	**m3/sn**	**25.11.2005**
2006 Su yılında anlık enaz akım	**:**	**0.000**	**m3/sn**	**05.10.2005**
Gözlem süresinde anlık ençok akım	**:**	**67.0**	**m3/sn**	**27.07.1983**
Gözlem süresinde anlık enaz akım	**:**	**0.000**	**m3/sn**	**30.10.1982**

Akımlar 01 Ekim 2005 'den 30 Eylül 2006' a kadar m3/sn olarak

Gün	Ekim	Kasım	Aralık	Ocak	Şubat	Mart	Nisan	Mayıs	Haziran	Temmuz	Ağustos	Eylül
01	KURU	1.17	0.384	6.08	0.420	2.75	0.240	0.017	0.001	0.001	0.001	0.080
02	KURU	1.42	0.384	2.48	0.775	2.75	0.200	0.017	0.001	0.001	0.001	0.034
03	KURU	1.08	0.384	1.60	0.925	3.50	0.150	0.009	0.001	0.001	0.001	0.013
04	KURU	0.532	0.312	1.33	1.17	3.05	0.150	0.009	0.001	0.001	0.001	0.007
05	KURU	0.384	0.312	1.08	1.42	2.00	0.150	0.009	0.001	0.001	0.003	0.003
06	KURU	0.532	0.240	1.80	1.60	1.08	0.110	0.009	0.001	0.001	0.003	0.003
07	KURU	0.700	0.240	3.95	1.08	0.476	0.080	0.013	0.001	0.001	0.003	0.004
08	KURU	1.00	0.200	4.28	0.850	0.925	0.080	0.110	0.003	0.001	0.009	0.004
09	KURU	0.850	0.240	3.35	0.700	1.33	0.080	0.240	0.050	0.007	0.004	0.007
10	KURU	0.348	0.220	2.75	0.850	1.25	0.080	0.060	0.532	0.004	0.003	0.022
11	KURU	0.150	0.200	1.80	1.42	2.75	0.080	0.027	0.027	0.003	0.003	0.013
12	KURU	0.150	0.150	0.925	1.50	6.08	0.080	0.027	0.004	0.003	0.003	0.009
13	KURU	0.080	0.130	0.775	1.25	2.90	0.080	0.040	0.040	0.003	0.003	0.009
14	KURU	0.150	0.110	1.00	1.17	1.50	0.060	0.027	1.25	0.003	0.003	0.009
15	KURU	0.850	0.080	0.925	1.17	1.33	0.060	0.017	0.130	0.003	0.003	0.009
16	KURU	0.644	0.080	0.532	1.00	1.17	0.060	0.017	0.022	0.003	0.003	0.009
17	KURU	0.588	0.080	0.312	1.42	1.08	0.060	0.017	0.004	0.003	0.003	0.009
18	KURU	0.588	0.095	0.312	9.40	0.925	0.060	0.013	0.004	0.003	0.003	0.009
19	0.825	1.70	0.240	1.42	7.28	1.17	0.060	0.009	0.001	0.003	0.003	0.009
20	6.62	5.18	0.476	1.50	7.76	1.42	0.060	0.009	0.001	0.003	0.003	0.009
21	1.80	2.24	0.476	1.25	4.46	1.00	0.040	0.009	0.001	0.003	0.003	0.009
22	0.312	1.25	0.532	1.08	3.05	0.700	0.040	0.009	0.001	0.003	0.003	0.009
23	0.130	1.60	0.588	0.850	2.60	0.588	0.040	0.004	0.001	0.003	0.003	0.009
24	0.070	8.80	0.588	0.588	2.60	0.850	0.027	0.004	0.001	0.003	0.003	0.009
25	0.060	10.8	0.588	0.588	2.36	0.850	0.027	0.004	0.001	0.003	0.003	0.009
26	0.040	7.04	0.588	0.588	3.80	0.700	0.027	0.004	0.001	0.003	0.003	0.040
27	0.040	2.24	1.00	0.588	3.05	0.476	0.027	0.004	0.001	0.003	0.003	0.034
28	0.040	1.08	5.90	0.850	2.75	0.384	0.027	0.004	0.001	0.003	0.009	0.013
29	0.070	0.588	7.52	1.08	-----	0.276	0.027	0.004	0.001	0.003	0.007	0.017
30	1.00	0.476	8.00	0.588	-----	0.240	0.027	0.004	0.001	0.003	0.003	0.130
31	1.60	-----	9.80	0.384	-----	0.240	-----	0.001	-----	0.001	0.022	-----
Maks.	7.52	11.5	11.5	6.26	11.5	8.00	0.240	0.312	2.60	0.009	0.034	0.150
Min.	KURU	0.080	0.060	0.240	0.384	0.240	0.027	0.001	0.001	0.001	0.001	0.003
Ortalama	0.407	1.81	1.29	1.50	2.42	1.48	0.076	0.024	0.069	0.003	0.004	0.018
LT/SN/Km2	9.73	43.2	31.0	36.0	58.0	35.3	1.83	0.576	1.66	0.062	0.093	0.439
AKIM mm.	26.1	112.	83.0	96.4	140.	94.5	4.73	1.54	4.31	0.165	0.250	1.14
MİL. M3	1.09	4.68	3.47	4.03	5.86	3.95	0.198	0.065	0.180	0.007	0.010	0.048

SU YILI (2006) YILLIK TOPLAM AKIM 23.59 MİLYON M3 564 MM. 17.9 LT/SN/Km2

13. Bati Karadeniz Havzasi

D13A048 ALAPLI Ç. ALAPLI

YERİ : **ZONGULDAK İLİ, ALAPLI İLÇE MERKEZİNİN 15 KM. GÜNEYİNDEDİR.**
31°23'0" Doğu - 41°9'0" Kuzey

YAĞIŞ ALANI : **245,00 km2** **YAKLAŞIK KOT : 20 m**

GÖZLEM SÜRESİ : **17.06.1983 - 30.09.2006**

ORTALAMA AKIMLAR : **Gözlem süresinde 6.182 m3/sn. (15 Yıllık) 2006 Su yılında 5.146 m3/sn.**

ANLIK EN ÇOK VE EN AZ AKIMLAR:

2006 Su yılında anlık ençok akım	:	**32.9**	**m3/sn**	**24.11.2005**
2006 Su yılında anlık enaz akım	:	**0.168**	**m3/sn**	**16.02.2006**
Gözlem süresinde anlık ençok akım	:	**106.**	**m3/sn**	**07.07.1991**
Gözlem süresinde anlık enaz akım	:	**0.000**	**m3/sn**	**08.10.1989**

Akımlar 01 Ekim 2005 'den 30 Eylül 2006' a kadar m3/sn olarak

Gün	Ekim	Kasım	Aralık	Ocak	Şubat	Mart	Nisan	Mayıs	Haziran	Temmuz	Ağustos	Eylül
01	1.02	8.71	6.67	16.0	7.18	15.1	5.88	1.92	1.10	1.10	0.585	2.84
02	1.02	7.44	6.16	12.9	7.95	15.1	5.88	1.92	1.10	0.980	0.585	2.08
03	1.43	6.42	6.42	10.8	7.95	22.0	5.16	1.92	1.10	0.980	0.585	1.23
04	1.57	5.75	6.16	9.83	7.44	21.0	5.16	1.76	0.980	0.901	0.585	0.901
05	1.15	6.67	9.83	9.83	7.18	15.1	4.80	1.76	0.980	0.901	0.585	0.743
06	1.02	8.71	7.44	9.53	7.95	12.3	4.54	1.60	0.901	0.822	0.544	0.664
07	1.02	9.22	6.16	16.9	7.69	10.3	4.54	1.60	0.980	0.822	0.544	0.743
08	1.02	9.53	5.91	16.9	7.18	13.0	4.02	2.08	0.980	0.901	0.585	0.664
09	0.880	7.95	6.42	12.9	6.67	13.0	4.54	3.76	1.23	0.901	0.585	0.664
10	0.880	6.67	5.75	10.4	8.71	11.6	4.54	2.40	1.35	0.822	0.585	0.743
11	0.880	6.16	5.42	8.97	4.80	14.4	4.28	1.92	1.48	0.743	0.544	0.743
12	1.43	5.75	5.26	7.95	1.92	21.0	4.28	1.76	1.48	0.743	0.544	0.743
13	1.29	5.58	5.09	7.18	0.503	20.1	4.02	2.84	1.60	0.743	0.544	0.664
14	1.57	5.58	4.93	6.67	0.324	17.4	3.76	2.24	5.52	0.743	0.585	0.664
15	1.71	6.16	4.76	6.16	0.222	13.7	4.02	1.92	2.40	0.743	0.585	0.585
16	2.17	5.75	5.42	5.91	0.168	11.6	3.50	1.92	1.76	0.743	0.585	0.585
17	4.27	5.58	6.67	5.75	0.204	10.3	3.06	1.60	1.48	0.743	0.544	0.544
18	3.31	6.16	6.42	5.75	1.60	9.60	3.06	1.60	1.23	0.822	0.544	0.585
19	4.40	6.16	7.44	7.69	13.0	11.6	3.06	1.60	1.10	0.743	0.585	0.585
20	21.7	12.3	7.18	8.97	23.0	10.3	2.84	1.48	0.980	0.743	0.585	0.585
21	13.8	16.6	6.67	8.71	22.0	9.60	2.84	1.48	0.980	0.664	0.544	0.585
22	8.97	13.5	6.16	8.46	20.1	9.00	2.84	1.48	1.10	0.664	0.585	0.664
23	6.67	12.6	6.16	8.71	17.4	8.40	2.62	1.35	0.980	0.743	0.585	0.664
24	5.75	29.2	5.91	8.20	15.8	10.3	2.62	1.35	0.980	0.743	0.585	0.585
25	5.42	27.6	5.91	7.69	14.4	9.00	2.40	1.35	0.980	0.743	0.544	0.980
26	5.09	22.1	6.67	7.18	16.5	7.80	2.40	1.23	0.901	0.664	0.544	1.35
27	4.76	15.7	8.97	6.67	19.2	6.60	2.24	1.76	0.901	0.664	0.503	0.901
28	4.60	12.3	23.4	6.42	15.8	6.60	2.08	1.60	0.980	0.585	0.544	0.664
29	5.09	9.53	20.8	6.16	-----	5.88	2.08	1.35	1.76	0.585	0.585	0.980
30	5.42	7.95	16.6	5.91	-----	6.60	1.92	1.23	1.35	0.585	0.585	7.20
31	6.16	-----	18.2	6.16	-----	5.88	-----	1.10	-----	0.585	0.664	-----
Maks.	24.4	32.9	27.6	21.7	27.0	25.0	5.88	4.02	9.00	1.10	0.743	11.6
Min.	0.880	5.42	4.76	5.58	0.168	5.88	1.92	1.10	0.901	0.544	0.503	0.544
Ortalama	4.05	10.3	8.10	8.94	9.39	12.1	3.63	1.77	1.35	0.770	0.570	1.07
LT/SN/Km2	16.5	42.1	33.0	36.5	38.3	49.3	14.8	7.23	5.53	3.14	2.33	4.37
AKIM mm.	44.2	109.	88.5	97.8	92.7	132.	38.4	19.4	14.3	8.42	6.24	11.3
MİL. M3	10.8	26.7	21.7	24.0	22.7	32.3	9.42	4.74	3.51	2.06	1.53	2.78

SU YILI (2006) YILLIK TOPLAM AKIM 162.24 MİLYON M3 662 MM. 21.0 LT/SN/Km2

13. Bati Karadeniz Havzasi

D13A049 ARIT Ç. DARIÖREN

YERİ : **BARTIN-AMASRA KARAYOLUNDAN 2 KM SONRA ARIT YOLUNA DÖNÜLÜR. AGİ ARIT YOLUNUN 20. KM.SİNDEDIR.**
32°34'17" Doğu - 41°40'43" Kuzey

YAĞIŞ ALANI : **137,00 km2** **YAKLAŞIK KOT : 230 m**

GÖZLEM SÜRESİ : **30.10.1983 - 30.09.2006**

ORTALAMA AKIMLAR : **Gözlem süresinde 3.920 m3/sn. (18 Yıllık) 2006 Su yılında 3.341 m3/sn.**

ANLIK EN ÇOK VE EN AZ AKIMLAR:

2006 Su yılında anlık ençok akım	:	**48.0**	**m3/sn**	**30.10.2005**
2006 Su yılında anlık enaz akım	:	**0.000**	**m3/sn**	**01.10.2005**
Gözlem süresinde anlık ençok akım	:	**222.**	**m3/sn**	**07.07.1991**
Gözlem süresinde anlık enaz akım	:	**0.000**	**m3/sn**	**01.10.1994**

Akımlar 01 Ekim 2005 'den 30 Eylül 2006' a kadar m3/sn olarak

Gün	Ekim	Kasım	Aralık	Ocak	Şubat	Mart	Nisan	Mayıs	Haziran	Temmuz	Ağustos	Eylül
01	KURU	20.6	4.03	11.8	1.92	17.4	2.99	0.560	0.322	0.322	KURU	KURU
02	KURU	8.30	3.86	7.48	2.71	15.6	2.99	0.483	0.322	0.322	KURU	KURU
03	KURU	5.43	12.8	5.66	2.31	31.3	2.85	0.483	0.322	0.293	KURU	KURU
04	KURU	3.70	5.43	6.34	2.44	13.4	2.31	0.483	0.322	0.264	KURU	KURU
05	KURU	3.12	8.57	5.66	2.44	8.30	2.17	0.483	0.293	0.264	KURU	KURU
06	KURU	3.53	5.03	5.88	3.26	6.80	2.09	0.483	0.264	0.264	KURU	KURU
07	KURU	4.03	3.70	7.75	3.39	7.02	2.09	0.483	0.264	0.264	KURU	KURU
08	KURU	3.39	3.26	12.4	2.71	8.02	2.00	0.642	0.264	0.264	KURU	KURU
09	KURU	3.12	3.26	7.02	2.44	7.48	2.00	8.02	0.264	0.264	KURU	KURU
10	KURU	2.17	2.58	5.20	4.53	6.34	1.92	2.71	0.322	0.264	KURU	KURU
11	KURU	1.75	2.17	4.37	14.8	9.11	1.63	0.943	0.410	0.264	KURU	KURU
12	KURU	1.34	2.09	3.70	6.57	8.02	1.56	0.826	0.439	0.264	KURU	KURU
13	KURU	1.24	1.92	2.85	4.87	9.11	1.44	0.766	0.601	0.264	KURU	KURU
14	KURU	1.56	1.50	2.17	4.03	7.75	1.44	0.766	3.86	0.264	KURU	KURU
15	KURU	6.57	1.34	2.00	3.26	6.80	1.24	0.725	2.00	0.264	KURU	KURU
16	0.212	4.53	1.50	1.83	2.99	5.43	1.13	0.601	0.766	0.240	KURU	KURU
17	4.03	2.31	4.03	1.69	2.85	3.86	0.943	0.483	0.461	0.240	KURU	KURU
18	3.86	2.17	2.99	1.63	15.6	3.12	0.886	0.483	0.439	0.175	KURU	KURU
19	4.37	2.17	7.02	4.20	24.4	3.39	0.886	0.483	0.381	0.175	KURU	KURU
20	29.1	3.70	4.70	4.53	22.7	3.12	0.766	0.483	0.381	0.175	KURU	KURU
21	13.1	11.8	4.20	2.71	18.8	2.99	0.684	0.461	0.352	0.175	KURU	KURU
22	5.43	8.57	4.03	2.44	14.8	3.39	0.642	0.461	0.322	0.175	KURU	KURU
23	3.26	7.25	3.53	2.58	13.4	3.39	0.601	0.461	0.322	0.175	KURU	KURU
24	1.56	15.2	3.12	2.09	12.4	6.11	0.601	0.439	0.322	0.175	KURU	KURU
25	1.44	28.7	2.99	1.69	12.8	5.03	0.581	0.439	0.322	0.175	KURU	0.322
26	1.44	21.0	3.86	1.69	20.6	4.03	0.560	0.439	0.322	0.212	KURU	3.26
27	1.24	13.8	4.87	1.69	15.9	2.99	0.560	0.439	0.322	0.212	KURU	0.684
28	1.19	10.5	15.6	1.56	12.1	2.85	0.560	0.439	0.322	0.212	KURU	0.352
29	9.11	7.48	14.8	1.44	-----	2.85	0.560	0.410	0.322	0.212	KURU	0.461
30	36.8	6.11	11.8	1.44	-----	3.12	0.560	0.352	0.322	0.212	KURU	12.1
31	17.9	-----	14.8	1.44	-----	3.12	-----	0.322	-----	0.212	KURU	-----
Maks.	48.0	32.6	24.0	14.1	37.3	36.8	2.99	14.8	4.87	0.322	KURU	25.7
Min.	KURU	1.24	1.24	1.44	1.69	2.71	0.560	0.322	0.264	0.175	KURU	KURU
Ortalama	4.32	7.17	5.33	4.03	8.97	7.14	1.37	0.840	0.532	0.234	KURU	0.573
LT/SN/Km2	31.6	52.3	38.9	29.4	65.4	52.1	10.0	6.13	3.88	1.71	0.000	4.18
AKIM mm.	84.5	136.	104.	78.8	158.	140.	26.0	16.4	10.1	4.58	0.000	10.8
MİL. M3	11.6	18.6	14.3	10.8	21.7	19.1	3.56	2.25	1.38	0.627	0.000	1.48

SU YILI (2006) YILLIK TOPLAM AKIM 105.40 MİLYON M3 769 MM. 24.4 LT/SN/Km2

13. Bati Karadeniz Havzasi

D13A050 İSPA Ç. ŞAMLIOĞLU

YERİ : **GERZE-SİNOP YOLUNUN GERZE'YE 6 KM MESAFESİNDEKİ ŞAMLIOĞLU KÖYÜNDEDİR. 25'LİK PAFTADAKİ YERİ : E34-A4**
35°2'54" Doğu - 41°50'57" Kuzey

YAĞIŞ ALANI : **17,00 km2** **YAKLAŞIK KOT : 85 m**

GÖZLEM SÜRESİ : **01.01.1983 - 30.09.2006**

ORTALAMA AKIMLAR : **Gözlem süresinde 0.211 m3/sn. (23 Yıllık) 2006 Su yılında 0.197 m3/sn.**

ANLIK EN ÇOK VE EN AZ AKIMLAR:

2006 Su yılında anlık ençok akım	**:**	**13.8**	**m3/sn**	**02.07.2006**
2006 Su yılında anlık enaz akım	**:**	**0.000**	**m3/sn**	**01.10.2005**
Gözlem süresinde anlık ençok akım	**:**	**25.4**	**m3/sn**	**26.10.1988**
Gözlem süresinde anlık enaz akım	**:**	**0.000**	**m3/sn**	**28.09.1984**

10. Anahtar Eğrisi (Seviyeler cm olarak)

Seviye	Akım	Seviye	Akım	Seviye	Akım	Seviye	Akım
1	0.001	61	3.0	119	9.9	209	26.3
17	0.217	72	4.1	134	12.1	233	31.9
28	0.642	83	5.3	150	14.7	257	38.3
39	1.3	95	6.7	168	18.0	283	46.1
50	2.1	106	8.1	188	21.9		

Akımlar 01 Ekim 2005 'den 30 Eylül 2006' a kadar m3/sn olarak

Gün	Ekim	Kasım	Aralık	Ocak	Şubat	Mart	Nisan	Mayıs	Haziran	Temmuz	Ağustos	Eylül
01	KURU	0.140	0.065	0.220	0.560	0.560	0.480	0.075	0.015	1.93	KURU	KURU
02	KURU	0.115	0.065	0.220	0.640	0.560	0.560	0.075	0.015	4.47	KURU	KURU
03	KURU	0.170	0.065	0.220	0.560	0.560	0.560	0.075	0.015	0.400	KURU	KURU
04	KURU	0.140	0.065	0.220	0.560	0.560	0.480	0.075	0.015	0.075	KURU	KURU
05	KURU	0.115	0.075	0.220	0.640	0.400	0.270	0.075	0.015	0.042	KURU	KURU
06	KURU	0.075	0.075	0.220	1.28	0.400	0.270	0.065	0.015	0.042	KURU	KURU
07	KURU	0.075	0.075	0.220	1.18	0.400	0.270	0.065	0.015	0.015	KURU	KURU
08	KURU	0.075	0.075	0.170	1.07	0.400	0.270	0.065	0.015	0.004	KURU	KURU
09	KURU	0.075	0.075	0.170	0.970	0.480	0.270	0.065	0.015	KURU	KURU	KURU
10	KURU	0.075	0.075	0.170	0.970	0.400	0.270	0.065	0.015	KURU	KURU	KURU
11	KURU	0.075	0.075	0.170	1.28	0.400	0.140	0.042	0.015	KURU	KURU	KURU
12	KURU	0.075	0.115	0.170	1.18	0.400	0.115	0.042	0.015	KURU	KURU	KURU
13	KURU	0.115	0.115	0.170	0.970	0.320	0.115	0.065	0.015	KURU	KURU	KURU
14	KURU	0.140	0.115	0.170	0.860	0.320	0.115	0.075	0.015	KURU	KURU	KURU
15	KURU	0.140	0.115	0.170	0.860	0.320	0.115	0.075	0.015	KURU	KURU	KURU
16	KURU	0.075	0.075	0.170	0.860	0.270	0.115	0.065	0.015	KURU	KURU	KURU
17	KURU	0.075	0.075	0.170	0.860	0.270	0.115	0.065	0.015	KURU	KURU	KURU
18	KURU	0.075	0.065	0.170	1.49	0.560	0.115	0.065	0.015	KURU	KURU	KURU
19	KURU	0.075	0.170	0.170	1.49	0.640	0.115	0.042	0.015	KURU	KURU	KURU
20	0.115	0.075	0.480	0.170	1.60	0.400	0.115	0.042	0.015	KURU	KURU	KURU
21	0.075	0.075	0.270	0.220	1.28	0.400	0.115	0.042	0.015	KURU	KURU	KURU
22	0.027	0.075	0.220	0.270	1.07	0.400	0.115	0.042	0.015	KURU	KURU	KURU
23	0.004	0.075	0.220	0.560	0.860	0.480	0.115	0.042	0.015	KURU	KURU	KURU
24	KURU	0.075	0.220	0.400	0.970	0.560	0.115	0.042	0.015	KURU	KURU	KURU
25	KURU	0.075	0.220	0.400	0.860	0.480	0.115	0.027	0.015	KURU	KURU	KURU
26	KURU	0.075	0.220	0.400	0.860	0.320	0.115	0.015	0.008	KURU	KURU	0.004
27	KURU	0.075	0.220	0.400	0.860	0.320	0.115	0.015	0.004	KURU	KURU	KURU
28	0.140	0.042	0.220	0.320	0.860	0.270	0.115	0.015	0.004	KURU	KURU	KURU
29	0.400	0.042	0.220	0.320	-----	0.270	0.115	0.015	0.004	KURU	KURU	KURU
30	0.720	0.042	0.220	0.320	-----	0.270	0.075	0.015	0.004	KURU	KURU	KURU
31	0.320	-----	0.220	0.320	-----	0.320	-----	0.008	-----	KURU	KURU	-----
Maks.	0.860	0.480	1.18	0.970	2.39	1.07	0.640	0.075	0.015	13.8	KURU	0.006
Min.	KURU	0.042	0.042	0.170	0.320	0.140	0.075	0.008	KURU	KURU	KURU	KURU
Ortalama	0.058	0.088	0.148	0.248	0.982	0.410	0.200	0.050	0.013	0.225	KURU	0.000
LT/SN/Km2	3.42	5.15	8.69	14.6	57.8	24.1	11.7	2.95	0.782	13.2	0.000	0.008
AKIM mm.	9.15	13.3	23.3	39.0	140.	64.6	30.4	7.91	2.03	35.5	0.000	0.020
MİL. M3	0.156	0.227	0.396	0.664	2.38	1.10	0.517	0.134	0.034	0.603	0.000	0.000

SU YILI (2006) YILLIK TOPLAM AKIM 6.21 MİLYON M3 365 MM. 11.6 LT/SN/Km2

13. Bati Karadeniz Havzasi

D13A052 KOCAÇAY CİDE

YERİ : CİDE BARTIN KARAYOLUNUN 5.KM SINDE, IRMAK-KUMLUCA KÖYLERİNİN OTASINDAN GEÇEN KOCAÇAY ÜZERİNDEDİR.
32°59'42" Doğu - 41°53'41" Kuzey

YAĞIŞ ALANI : 2303,50 km2 **YAKLAŞIK KOT** : 20 m

GÖZLEM SÜRESİ : 11.08.1984 - 30.09.2006

ORTALAMA AKIMLAR : Gözlem süresinde 26.596 m3/sn. (16 Yıllık) 2006 Su yılında 19.734 m3/sn.

ANLIK EN ÇOK VE EN AZ AKIMLAR:

2006 Su yılında anlık ençok akım	:	286.	m3/sn	03.03.2006
2006 Su yılında anlık enaz akım	:	1.22	m3/sn	09.10.2005
Gözlem süresinde anlık ençok akım	:	960.	m3/sn	28.02.1989
Gözlem süresinde anlık enaz akım	:	0.000	m3/sn	01.10.1999

2011. Anahtar Eğrisi (Seviyeler cm olarak)

Seviye	Akım	Seviye	Akım	Seviye	Akım	Seviye	Akım
1	0.079	96	20.2	191	313.	289	2015.
20	0.541	115	39.0	211	477.	309	2775.
39	1.7	134	71.7	230	702.	329	3833.
58	4.2	153	123.	248	990.	352	5380.
77	9.5	172	199.	270	1459.	374	7450.

Akımlar 01 Ekim 2005 'den 30 Eylül 2006' a kadar m3/sn olarak

Gün	Ekim	Kasım	Aralık	Ocak	Şubat	Mart	Nisan	Mayıs	Haziran	Temmuz	Ağustos	Eylül
01	1.63	41.7	25.5	74.3	12.0	144.	16.0	3.40	4.08	3.26	2.28	1.95
02	1.49	30.6	20.6	45.0	10.7	142.	15.1	3.40	4.08	3.26	2.12	2.12
03	1.49	19.7	27.5	33.6	9.99	188.	15.1	3.40	4.08	3.05	2.12	2.12
04	1.49	13.3	29.6	33.6	10.7	142.	13.3	2.99	4.08	3.05	2.12	1.95
05	1.49	14.2	35.0	34.3	12.0	92.3	12.6	2.99	3.87	2.90	2.12	1.95
06	1.49	16.9	27.5	55.0	16.0	74.3	11.3	2.99	4.08	2.90	1.95	2.28
07	1.36	18.8	20.6	75.7	18.8	72.9	10.7	2.99	4.08	2.90	1.95	2.28
08	1.36	16.9	16.9	65.8	15.1	77.1	10.7	3.40	3.87	2.90	1.78	2.12
09	1.36	14.2	15.1	45.0	16.9	80.5	10.7	9.16	4.08	2.90	1.78	2.12
10	1.36	10.7	13.3	33.0	19.7	65.8	9.33	13.3	4.64	2.90	1.78	2.12
11	1.22	8.67	12.0	27.5	78.5	67.2	9.33	8.41	4.64	2.90	1.78	1.95
12	1.36	7.34	10.7	23.4	46.6	72.9	8.67	7.66	6.12	2.90	1.61	1.95
13	1.36	6.27	9.99	20.6	32.3	75.7	8.67	9.16	5.37	2.90	1.61	1.95
14	1.36	8.00	9.33	18.8	26.5	70.1	8.00	18.4	8.78	2.90	1.61	1.95
15	1.63	58.3	8.67	16.9	23.4	58.3	7.34	14.5	12.1	2.90	1.44	1.95
16	1.49	33.6	8.67	15.1	19.7	45.0	6.68	9.53	7.27	2.59	1.44	1.95
17	2.99	21.5	12.0	13.3	17.9	35.0	6.27	8.41	6.12	2.59	1.44	1.95
18	3.81	14.2	9.33	12.0	61.6	33.0	5.86	7.66	5.37	2.59	1.44	1.95
19	5.86	10.7	24.4	16.0	131.	33.0	5.45	7.27	4.64	2.59	1.61	1.95
20	78.5	16.0	23.4	22.4	118.	31.6	5.45	6.89	4.28	2.43	1.61	2.12
21	50.0	67.2	16.9	13.3	114.	28.5	5.04	6.12	4.28	2.43	1.61	2.12
22	24.4	36.7	13.3	14.2	112.	26.5	5.04	5.73	4.08	2.59	1.61	2.12
23	12.6	28.5	13.3	14.2	104.	28.5	4.63	5.73	4.08	2.90	1.61	2.12
24	8.00	40.0	12.6	12.0	100.	34.3	4.63	5.37	3.87	2.90	1.61	2.12
25	6.68	80.5	12.6	9.99	102.	32.3	4.22	5.37	3.87	2.74	1.44	2.43
26	5.04	94.3	16.0	10.7	163.	25.5	3.81	5.01	3.67	2.74	1.61	2.74
27	4.22	70.1	17.9	9.99	150.	21.5	3.81	5.01	3.67	2.74	1.61	2.59
28	4.63	56.6	48.3	9.33	120.	19.7	3.40	5.01	3.46	2.59	1.61	2.59
29	55.0	38.3	58.3	8.00	-----	17.9	3.40	4.64	3.67	2.43	1.61	2.59
30	110.	33.0	50.0	8.00	-----	17.9	3.40	4.64	3.67	2.43	1.61	9.16
31	67.2	-----	67.2	8.00	-----	17.9	-----	4.28	-----	2.43	1.61	-----
Maks.	137.	112.	122.	112.	186.	286.	16.9	26.6	14.5	3.46	2.43	40.9
Min.	1.22	5.45	8.00	7.34	8.67	16.9	3.40	2.99	3.46	2.43	1.44	1.78
Ortalama	14.9	30.9	22.1	25.8	59.4	60.4	7.93	6.54	4.80	2.78	1.71	2.38
LT/SN/Km2	6.47	13.4	9.61	11.2	25.8	26.2	3.44	2.84	2.08	1.21	0.744	1.03
AKIM mm.	17.3	34.8	25.7	30.0	62.4	70.2	8.92	7.61	5.40	3.23	1.99	2.67
MİL. M3	39.9	80.1	59.3	69.0	144.	162.	20.6	17.5	12.4	7.45	4.59	6.16

SU YILI (2006) YILLIK TOPLAM AKIM 623.00 MİLYON M3 270 MM. 8.6 LT/SN/Km2

13. Bati Karadeniz Havzasi

D13A053 ARAÇ Ç. KAYABOĞAZI

YERİ : **KASTAMONU İSTANBUL KARAYOLUNUN 90.KM SİNDE YEŞILOVA KÖYÜNDEKİ TOPRAKSU REGÜLATÖRÜ ÜZERİNDEDİR.**
33°1'32" Doğu - 41°13'51" Kuzey

YAĞIŞ ALANI : **1747,00 km2** **YAKLAŞIK KOT : 460 m**

GÖZLEM SÜRESİ : **04.09.1984 - 30.09.2006**

ORTALAMA AKIMLAR : **Gözlem süresinde 8.497 m3/sn. (16 Yıllık) 2006 Su yılında 6.967 m3/sn.**

ANLIK EN ÇOK VE EN AZ AKIMLAR:

2006 Su yılında anlık ençok akım	**:**	**66.8**	**m3/sn**	**03.03.2006**
2006 Su yılında anlık enaz akım	**:**	**0.000**	**m3/sn**	**28.08.2006**
Gözlem süresinde anlık ençok akım	**:**	**241.**	**m3/sn**	**04.06.2000**
Gözlem süresinde anlık enaz akım	**:**	**0.000**	**m3/sn**	**04.07.1994**

Akımlar 01 Ekim 2005 'den 30 Eylül 2006' a kadar m3/sn olarak

Gün	Ekim	Kasım	Aralık	Ocak	Şubat	Mart	Nisan	Mayıs	Haziran	Temmuz	Ağustos	Eylül
01	2.04	2.22	5.16	6.92	3.06	43.1	17.0	8.92	2.40	1.68	0.024	0.109
02	1.68	2.22	4.54	5.88	3.06	39.2	17.5	11.2	2.40	1.50	0.015	0.067
03	2.22	2.04	4.28	5.16	3.06	45.8	15.0	11.2	2.22	1.23	0.009	0.222
04	2.22	2.22	4.02	4.80	3.06	44.2	13.6	9.28	2.22	0.746	0.011	0.191
05	2.04	2.22	4.02	4.54	4.80	34.4	12.4	8.56	1.68	0.524	0.011	0.291
06	1.86	2.22	4.02	4.80	6.24	30.5	12.4	7.56	1.50	0.450	0.015	0.253
07	1.68	2.40	3.76	7.56	7.24	29.9	13.2	12.4	1.36	0.408	0.019	0.222
08	1.50	2.40	3.50	9.28	7.24	34.4	15.0	18.0	2.40	0.672	0.019	0.191
09	1.50	2.40	3.28	8.20	7.24	38.1	17.0	15.0	3.06	0.598	0.015	0.162
10	1.50	2.40	3.06	7.24	6.92	28.6	16.0	12.4	5.16	0.408	0.013	0.162
11	1.50	2.22	3.06	5.88	11.2	31.8	19.0	12.4	4.28	0.240	0.019	0.291
12	1.50	2.22	2.84	5.16	13.6	31.8	18.5	10.8	4.54	0.165	0.039	0.253
13	1.50	2.04	2.84	4.54	10.0	29.9	16.0	15.5	3.28	0.111	0.039	0.133
14	1.50	2.04	2.62	4.28	9.28	28.6	16.0	22.5	4.54	0.096	0.039	0.109
15	1.50	2.62	2.62	4.02	8.56	28.6	17.5	17.5	3.50	0.125	0.051	0.085
16	1.50	2.62	2.62	3.50	6.92	23.5	15.0	15.0	3.06	0.082	0.051	0.133
17	1.50	2.62	2.84	3.28	7.88	21.5	12.0	12.4	2.62	0.096	0.067	0.085
18	1.50	2.40	3.06	3.28	10.0	20.0	10.4	10.4	2.04	0.053	0.067	0.067
19	1.50	2.40	3.28	3.28	24.7	21.5	11.2	8.92	1.86	0.053	0.067	0.162
20	2.40	3.06	3.50	3.50	32.5	20.0	9.64	8.20	1.50	0.045	0.085	0.162
21	3.28	6.92	3.06	3.28	33.8	22.5	10.0	7.56	1.23	0.036	0.067	0.437
22	3.06	5.52	2.62	3.28	37.6	19.5	9.64	6.92	1.36	0.024	0.051	0.513
23	2.62	4.28	2.84	3.28	35.7	22.0	8.56	5.88	1.23	0.053	0.051	0.735
24	2.22	4.02	3.06	3.06	36.4	29.9	8.20	5.16	1.09	0.672	0.109	0.801
25	2.04	4.80	3.06	2.84	39.8	30.5	6.92	4.54	0.956	0.215	0.109	1.24
26	1.86	7.56	2.84	2.84	52.9	22.5	5.88	4.54	0.672	0.111	0.067	1.05
27	1.86	7.24	2.62	3.06	53.6	17.5	5.16	4.80	0.524	0.082	0.085	1.05
28	1.86	6.92	2.84	3.06	44.7	16.0	4.80	4.28	0.746	0.045	0.109	1.15
29	1.86	6.24	3.28	2.40	-----	16.0	5.16	3.76	1.36	0.045	0.051	1.53
30	1.86	5.88	3.76	2.62	-----	17.0	6.60	3.28	1.36	0.030	0.085	1.62
31	2.04	-----	4.28	2.40	-----	19.0	-----	2.62	-----	0.015	0.109	-----
Maks.	3.50	7.88	5.16	10.0	53.6	66.8	22.5	27.3	8.20	3.06	0.109	1.94
Min.	1.36	2.04	2.40	2.40	3.06	11.6	2.62	1.23	0.240	0.002	KURU	KURU
Ortalama	1.89	3.55	3.33	4.43	18.6	27.7	12.2	9.73	2.20	0.342	0.051	0.449
LT/SN/Km2	1.08	2.03	1.91	2.53	10.7	15.8	6.97	5.57	1.26	0.196	0.029	0.257
AKIM mm.	2.90	5.26	5.10	6.79	25.8	42.4	18.1	14.9	3.27	0.525	0.078	0.666
MİL. M3	5.07	9.19	8.91	11.9	45.0	74.1	31.6	26.0	5.72	0.917	0.135	1.16

SU YILI (2006) YILLIK TOPLAM AKIM 219.70 MİLYON M3 126 MM. 4.0 LT/SN/Km2

13. Bati Karadeniz Havzasi

D13A055 KARACA S. KUYUMCULU

YERİ : ADAPAZARI-KUYUMCULU KÖYÜNDEDİR. 68.KM ASFALTBATI KARADENİZ SUYU.
30°47'17" Doğu - 41°3'40" Kuzey

YAĞIŞ ALANI : 136.01 km2 **YAKLAŞIK KOT :** 10.0080 m

GÖZLEM SÜRESİ : 01.12.1988 - 30.09.2006

ORTALAMA AKIMLAR : Gözlem süresinde 5.259 m3/sn. (12 Yıllık) 2006 Su yılında 5.054 m3/sn.

ANLIK EN ÇOK VE EN AZ AKIMLAR:

2006 Su yılında anlık ençok akım	:	115.	m3/sn	21.11.2005
2006 Su yılında anlık enaz akım	:	0.205	m3/sn	21.08.2006
Gözlem süresinde anlık ençok akım	:	128.	m3/sn	13.07.2002
Gözlem süresinde anlık enaz akım	:	0.012	m3/sn	30.12.1989

Akımlar 01 Ekim 2005 'den 30 Eylül 2006' a kadar m3/sn olarak

Gün	Ekim	Kasım	Aralık	Ocak	Şubat	Mart	Nisan	Mayıs	Haziran	Temmuz	Ağustos	Eylül
01	0.216	8.94	22.5	7.85	4.75	14.6	1.27	1.05	0.781	0.350	0.248	0.227
02	0.227	5.19	20.8	6.30	5.19	13.0	2.87	0.994	0.728	0.333	0.248	0.227
03	0.227	3.87	20.4	5.19	5.41	17.3	2.64	0.994	0.728	0.315	0.248	0.237
04	0.227	6.52	19.6	4.57	5.41	14.9	2.52	0.994	0.728	0.315	0.248	0.248
05	0.248	6.96	19.6	4.04	5.64	10.4	2.52	0.994	0.728	0.315	0.248	0.248
06	0.259	6.96	19.6	3.69	6.74	8.10	2.41	0.994	0.728	0.315	0.248	0.259
07	0.269	10.3	18.9	5.41	7.85	6.66	2.29	0.940	0.781	0.315	0.248	0.259
08	0.259	8.39	17.7	10.8	7.41	8.67	2.18	0.940	0.781	0.315	0.248	0.259
09	2.52	5.64	17.3	8.39	6.96	12.7	2.18	1.05	0.781	0.315	0.248	0.259
10	1.25	4.22	16.1	6.96	8.12	8.96	2.06	0.994	0.834	0.315	0.248	0.259
11	0.781	3.16	16.5	5.86	26.9	11.2	2.06	0.887	0.834	0.298	0.248	0.248
12	0.568	2.75	19.6	5.64	14.9	19.0	1.95	0.887	0.781	0.298	0.248	0.259
13	1.10	2.75	20.0	12.2	10.6	16.0	1.83	1.39	0.940	0.298	0.248	0.259
14	1.25	4.04	9.48	14.9	8.67	11.5	1.76	1.17	1.78	0.298	0.237	0.259
15	1.25	10.6	3.69	11.9	7.19	8.96	1.68	0.994	0.711	0.280	0.237	0.259
16	1.39	7.63	4.04	8.94	6.52	7.24	1.61	0.887	0.540	0.280	0.248	0.259
17	1.39	5.64	6.30	7.19	6.30	5.22	1.61	0.887	0.455	0.280	0.248	0.259
18	1.47	5.19	5.41	5.86	13.8	4.65	1.54	0.887	0.420	0.280	0.237	0.259
19	1.47	5.41	8.12	6.08	21.2	4.94	1.54	0.887	0.368	0.280	0.237	0.259
20	1.47	18.1	6.74	8.12	22.5	4.65	1.39	0.834	0.368	0.280	0.237	0.259
21	1.76	65.4	5.41	6.74	21.2	3.84	1.32	0.781	0.350	0.280	0.227	0.259
22	1.68	36.2	4.75	6.30	19.6	3.32	1.25	0.781	0.350	0.280	0.227	0.259
23	1.68	29.2	4.57	7.41	19.3	3.07	1.25	0.781	0.350	0.269	0.227	0.259
24	1.25	42.7	4.57	6.74	17.7	3.07	1.25	0.674	0.350	0.269	0.227	0.259
25	0.940	46.0	4.22	5.86	15.7	2.81	1.17	0.621	0.350	0.269	0.227	0.259
26	0.887	46.0	4.97	5.64	20.4	1.95	1.17	0.621	0.350	0.269	0.227	0.280
27	0.834	35.3	6.74	4.75	19.6	1.78	1.17	0.674	0.333	0.269	0.227	0.280
28	0.781	29.2	12.2	4.40	16.1	1.69	1.10	0.674	0.333	0.259	0.227	0.280
29	1.25	26.5	11.9	4.40	-----	1.52	1.10	0.674	0.540	0.259	0.227	0.298
30	6.30	24.8	9.48	4.22	-----	1.52	1.10	0.728	0.420	0.259	0.227	0.569
31	7.19	-----	8.67	4.22	-----	1.35	-----	0.781	-----	0.259	0.227	-----
Maks.	11.4	115.	30.0	17.3	37.2	22.5	2.87	1.68	7.52	0.368	0.259	1.44
Min.	0.216	2.64	3.33	3.51	4.75	1.35	1.10	0.621	0.333	0.259	0.205	0.227
Ortalama	1.37	17.1	11.9	6.79	12.6	7.57	1.73	0.885	0.617	0.291	0.239	0.269
LT/SN/Km2	10.1	126.	87.7	49.9	92.3	55.6	12.7	6.51	4.54	2.14	1.76	1.98
AKIM mm.	26.9	326.	235.	134.	223.	149.	32.9	17.4	11.8	5.73	4.70	5.12
MİL. M3	3.66	44.4	32.0	18.2	30.4	20.3	4.47	2.37	1.60	0.779	0.640	0.697

SU YILI (2006) YILLIK TOPLAM AKIM 159.52 MİLYON M3 1173 MM. 37.2 LT/SN/Km2

13. Bati Karadeniz Havzasi

D13A059 B.MELEN Ç. UĞURLUKÖY

YERİ : **DÜZCE AKÇAKOCA SAHİL YOLUNDAN 28 KM SONRA UĞURLU KÖYÜ İSTİKAMETİNE DOĞRU SAPILIR İSTASYON KÖY İÇİNDEKİ KÖPRÜ ÜZERİNDEDİR. PAFTA: 25.000 EREĞ-F25-C3 30°59'54" Doğu - 41°1'51" Kuzey**

YAĞIŞ ALANI : **2317,00 km2** **YAKLAŞIK KOT : 10 m**

GÖZLEM SÜRESİ : **20.09.1996 - 30.09.2006**

ORTALAMA AKIMLAR : **Gözlem süresinde 49.819 m3/sn. (9 Yıllık) 2006 Su yılında 44.803 m3/sn.**

ANLIK EN ÇOK VE EN AZ AKIMLAR:

2006 Su yılında anlık ençok akım	**:**	**223.**	**m3/sn**	**20.11.2005**
2006 Su yılında anlık enaz akım	**:**	**3.31**	**m3/sn**	**21.08.2006**
Gözlem süresinde anlık ençok akım	**:**	**405.**	**m3/sn**	**14.08.1997**
Gözlem süresinde anlık enaz akım	**:**	**3.31**	**m3/sn**	**21.08.2006**

İstasyon için kullanılmış anahtar bulunamadı.

Akımlar 01 Ekim 2005 'den 30 Eylül 2006' a kadar m3/sn olarak

Gün	Ekim	Kasım	Aralık	Ocak	Şubat	Mart	Nisan	Mayıs	Haziran	Temmuz	Ağustos	Eylül
01	6.92	31.1	99.0	84.6	58.4	125.	65.4	30.4	15.2	14.2	5.96	5.00
02	6.92	25.5	84.6	73.8	62.6	119.	62.6	29.0	12.9	11.6	5.96	13.3
03	7.24	26.9	80.4	66.8	58.4	152.	61.9	29.0	9.88	11.6	5.32	8.62
04	8.20	26.2	73.8	64.0	59.8	159.	70.3	28.3	9.04	19.0	5.32	7.24
05	8.20	17.5	74.5	63.3	60.5	134.	69.6	28.3	8.20	15.2	5.00	5.96
06	7.56	40.9	68.2	66.1	64.7	119.	68.9	27.6	9.46	13.3	5.00	5.96
07	6.92	74.5	61.9	90.0	69.6	112.	68.2	27.6	12.4	12.9	4.71	5.96
08	7.24	78.0	57.7	109.	66.1	116.	70.3	26.9	12.9	12.0	5.00	5.64
09	6.28	54.2	55.6	87.6	66.8	130.	73.1	30.4	16.5	11.1	5.64	5.96
10	6.92	47.9	54.2	75.9	79.8	125.	70.3	29.7	18.0	11.1	5.00	5.64
11	6.60	38.8	52.8	68.9	172.	132.	68.2	24.8	14.7	10.3	4.71	5.64
12	11.1	34.6	51.4	65.4	124.	150.	67.5	22.7	15.2	10.3	4.71	5.96
13	10.7	32.5	50.7	95.4	103.	143.	63.3	36.7	13.8	9.46	4.71	5.96
14	9.46	35.3	48.6	85.8	87.6	131.	61.2	46.5	42.3	9.88	4.42	5.64
15	11.1	39.5	47.9	71.0	79.8	119.	57.7	34.6	21.0	9.04	4.13	5.32
16	12.4	38.8	52.1	64.0	75.2	107.	54.9	29.0	17.5	8.20	3.84	5.00
17	13.8	36.0	66.8	58.4	74.5	97.2	52.8	26.2	15.6	7.88	3.55	4.71
18	15.6	37.4	55.6	53.5	105.	90.0	40.9	24.1	14.2	8.62	4.13	4.42
19	12.4	38.8	62.6	54.9	134.	96.0	35.3	22.0	13.3	8.20	3.84	4.42
20	45.8	84.0	64.7	71.0	145.	91.2	34.6	21.5	12.0	7.56	3.84	4.42
21	73.8	146.	61.9	62.6	135.	86.4	31.8	20.5	9.88	7.56	3.55	4.71
22	40.2	91.8	56.3	64.0	122.	82.2	30.4	19.5	9.46	7.24	3.84	5.32
23	29.7	84.0	55.6	67.5	118.	83.4	27.6	19.5	13.3	7.56	4.13	5.64
24	24.8	146.	52.1	62.6	114.	92.4	28.3	20.0	12.0	7.56	3.84	5.64
25	16.5	168.	50.7	59.8	116.	92.4	34.6	19.5	11.6	7.24	3.84	8.20
26	13.8	178.	60.5	58.4	136.	84.0	26.2	19.0	11.1	6.92	3.55	7.56
27	12.9	165.	70.3	56.3	139.	78.6	31.1	19.0	11.1	6.60	3.84	6.28
28	11.6	149.	96.6	56.3	130.	75.9	31.1	19.0	11.1	6.60	3.84	5.64
29	12.9	131.	97.2	56.3	-----	74.5	29.7	18.0	40.9	6.28	4.42	6.28
30	22.7	115.	86.4	54.9	-----	72.4	31.8	17.5	18.0	5.96	4.42	9.04
31	27.6	-----	83.4	55.6	-----	73.8	-----	15.6	-----	5.96	4.42	-----
Maks.	85.8	223.	107.	119.	205.	181.	74.5	57.0	153.	21.5	6.28	18.0
Min.	6.28	17.0	47.9	50.7	54.2	69.6	23.4	15.2	7.88	5.96	3.31	4.42
Ortalama	16.4	73.7	65.6	68.5	98.5	108.	50.7	25.2	15.1	9.58	4.47	6.17
LT/SN/Km2	7.07	31.8	28.3	29.6	42.5	46.5	21.9	10.9	6.51	4.13	1.93	2.66
AKIM mm.	18.9	82.5	75.9	79.2	103.	125.	56.7	29.2	16.9	11.1	5.16	6.90
MİL. M3	43.9	191.	176.	183.	238.	289.	131.	67.6	39.1	25.7	12.0	16.0

SU YILI (2006) YILLIK TOPLAM AKIM 1412.30 MİLYON M3 610 MM. 19.3 LT/SN/Km2

13. Bati Karadeniz Havzasi

D13A060 BAŞKÖY D. BAŞKÖY

YERİ : **KASTAMONU İLI ARAÇ VE İHSANGAZI İLÇELERİ ARASINDAKİ KARAYOLUNUN 5.3 KM SINDE BAŞKÖY DERESI ÜZERINDEKI KARAYOLU KÖPRÜSÜNDEDİR.**
33°23'0" Doğu - 41°13'0" Kuzey

YAĞIŞ ALANI : **141,20 km2** **YAKLAŞIK KOT : 685 m**

GÖZLEM SÜRESİ : **01.01.2000 - 30.09.2006**

ORTALAMA AKIMLAR : **Gözlem süresinde 0.917 m3/sn. (2 Yıllık) 2006 Su yılında 0.742 m3/sn.**

ANLIK EN ÇOK VE EN AZ AKIMLAR:

2006 Su yılında anlık ençok akım	:	**6.57**	**m3/sn**	**24.03.2006**
2006 Su yılında anlık enaz akım	:	**0.003**	**m3/sn**	**04.08.2006**
Gözlem süresinde anlık ençok akım	:	**160.0**	**m3/sn**	**26.12.2001**
Gözlem süresinde anlık enaz akım	:	**0.000**	**m3/sn**	**19.08.2005**

Akımlar 01 Ekim 2005 'den 30 Eylül 2006' a kadar m3/sn olarak

Gün	Ekim	Kasım	Aralık	Ocak	Şubat	Mart	Nisan	Mayıs	Haziran	Temmuz	Ağustos	Eylül
01	0.106	0.225	0.695	1.93	0.186	0.621	2.80	1.18	0.248	0.248	0.018	0.044
02	0.106	0.225	0.546	1.56	0.106	0.695	2.80	1.59	0.248	0.212	0.018	0.387
03	0.186	0.225	0.546	0.695	0.070	1.18	2.35	2.35	0.318	0.176	0.018	0.176
04	0.225	0.225	0.411	0.621	0.070	4.01	2.11	1.59	0.248	0.176	0.018	0.130
05	0.186	0.225	0.411	0.621	0.106	3.59	1.94	1.32	0.248	0.130	0.018	0.078
06	0.147	0.264	0.411	0.621	0.070	3.17	1.94	1.06	0.248	0.130	0.018	0.063
07	0.147	0.329	0.411	0.695	0.106	3.38	2.11	1.06	0.248	0.130	0.018	0.063
08	0.147	0.329	0.411	0.818	0.225	3.59	2.58	1.18	0.318	0.176	0.018	0.044
09	0.106	0.264	0.411	0.695	0.621	3.59	2.35	1.59	0.681	0.176	0.018	0.044
10	0.106	0.264	0.329	0.695	0.546	3.17	2.35	2.11	0.608	0.130	0.018	0.044
11	0.106	0.264	0.329	0.695	0.818	2.96	2.58	1.76	0.387	0.130	0.044	0.044
12	0.147	0.225	0.329	0.621	1.18	2.75	1.94	1.45	0.387	0.130	0.044	0.044
13	0.147	0.225	0.329	0.546	0.941	3.17	1.59	2.34	0.318	0.130	0.044	0.044
14	0.147	0.225	0.329	0.546	0.941	4.01	1.45	2.75	0.318	0.078	0.044	0.044
15	0.147	0.264	0.329	0.546	0.818	4.64	1.76	1.85	0.318	0.078	0.044	0.044
16	0.147	0.329	0.329	0.411	0.621	3.80	1.32	1.30	0.318	0.078	0.044	0.044
17	0.147	0.264	0.411	0.411	0.621	3.38	1.06	0.991	0.318	0.078	0.018	0.044
18	0.186	0.264	0.329	0.329	0.411	2.96	0.941	0.754	0.248	0.078	0.018	0.044
19	0.147	0.264	0.546	0.411	1.18	2.96	0.941	0.681	0.248	0.078	0.018	0.044
20	0.225	0.329	0.546	0.546	1.59	3.17	0.818	0.608	0.248	0.063	0.018	0.044
21	0.225	0.411	0.546	0.546	1.94	3.80	0.818	0.535	0.212	0.063	0.018	0.044
22	0.225	0.411	0.546	0.546	2.58	3.80	0.695	0.387	0.212	0.063	0.003	0.130
23	0.225	0.411	0.546	0.411	2.35	4.64	0.695	0.387	0.212	0.078	0.018	0.176
24	0.186	0.411	0.546	0.411	2.35	6.10	0.695	0.318	0.176	0.176	0.018	0.176
25	0.186	0.546	0.546	0.411	2.35	4.89	0.695	0.318	0.176	0.078	0.018	0.176
26	0.147	0.818	0.546	0.329	1.45	3.23	0.695	0.318	0.176	0.078	0.018	0.212
27	0.147	1.06	0.546	0.264	0.941	2.80	0.621	0.318	0.130	0.044	0.044	0.212
28	0.186	0.941	0.411	0.225	0.695	2.58	0.621	0.318	0.176	0.044	0.044	0.176
29	0.225	0.818	0.411	0.225	-----	2.58	0.621	0.318	0.212	0.044	0.044	0.176
30	0.225	0.818	0.411	0.225	-----	3.01	0.695	0.318	0.318	0.044	0.044	0.176
31	0.225	-----	1.21	0.225	-----	3.23	-----	0.248	-----	0.044	0.044	-----
Maks.	0.329	1.06	1.73	1.93	3.01	6.57	3.46	4.79	2.34	0.608	0.044	0.608
Min.	0.106	0.225	0.329	0.225	0.070	0.621	0.621	0.248	0.130	0.044	0.003	0.018
Ortalama	0.168	0.396	0.473	0.575	0.924	3.27	1.49	1.07	0.284	0.108	0.027	0.106
LT/SN/Km2	1.19	2.80	3.35	4.07	6.55	23.2	10.5	7.61	2.01	0.768	0.189	0.748
AKIM mm.	3.19	7.27	8.97	10.9	15.8	62.1	27.3	20.4	5.21	2.06	0.507	1.94
MİL. M3	0.450	1.03	1.27	1.54	2.24	8.77	3.85	2.88	0.736	0.290	0.072	0.274

SU YILI (2006) YILLIK TOPLAM AKIM 23.40 MİLYON M3 166 MM. 5.3 LT/SN/Km2

13. Bati Karadeniz Havzasi

D13A061 ARAÇ Ç. ARAÇ

YERİ : **KASTAMONU'NUN ARAÇ İLÇESI MERKEZINDEKİ KARAYOLU KÖPRÜSÜNÜN 300 METRE MENBASINDADIR**
33°19'41" Doğu - 41°14'21" Kuzey

YAĞIŞ ALANI : **885,50 km2** **YAKLAŞIK KOT : 620 m**

GÖZLEM SÜRESİ : **03.08.2000 - 30.09.2006**

ORTALAMA AKIMLAR : **Gözlem süresinde 6.243 m3/sn. (4 Yıllık) 2006 Su yılında 3.344 m3/sn.**

ANLIK EN ÇOK VE EN AZ AKIMLAR:

2006 Su yılında anlık ençok akım	:	**23.9**	**m3/sn**	**03.03.2006**
2006 Su yılında anlık enaz akım	:	**0.010**	**m3/sn**	**24.09.2006**
Gözlem süresinde anlık ençok akım	:	**169.**	**m3/sn**	**15.05.2001**
Gözlem süresinde anlık enaz akım	:	**0.000**	**m3/sn**	**15.05.2001**

Akımlar 01 Ekim 2005 'den 30 Eylül 2006' a kadar m3/sn olarak

Gün	Ekim	Kasım	Aralık	Ocak	Şubat	Mart	Nisan	Mayıs	Haziran	Temmuz	Ağustos	Eylül
01	0.730	1.32	3.25	4.48	1.92	11.5	8.00	5.43	2.74	2.40	1.64	0.141
02	0.730	1.20	2.91	3.59	1.68	10.5	7.67	6.00	2.57	1.56	1.64	2.94
03	1.80	1.20	2.74	3.42	1.68	13.0	7.33	7.33	2.40	1.20	1.31	1.31
04	1.32	1.20	2.74	3.42	1.68	12.0	6.33	5.62	2.28	1.11	1.14	0.816
05	0.730	1.32	2.57	3.08	1.80	8.75	6.00	5.05	2.04	1.01	1.14	0.488
06	0.598	1.32	2.40	3.42	1.92	8.00	6.00	4.86	2.04	0.824	0.980	0.324
07	0.532	1.56	2.28	3.59	2.28	8.25	6.33	9.00	2.04	0.824	0.980	0.324
08	0.532	1.32	2.16	3.76	2.16	9.50	7.67	11.0	3.42	0.918	0.980	0.324
09	0.532	1.32	2.04	3.42	2.16	10.5	8.00	8.50	3.76	0.918	0.816	0.160
10	0.532	1.11	1.92	3.25	2.04	8.25	8.50	7.33	4.10	0.824	0.324	0.488
11	0.532	1.01	1.92	2.91	3.08	8.25	11.0	6.67	3.42	0.824	0.160	0.488
12	0.598	0.918	1.92	2.74	3.42	9.00	8.75	6.33	3.42	0.824	0.324	0.488
13	0.664	0.918	1.68	2.57	2.91	11.5	8.75	9.50	2.91	0.664	0.324	0.652
14	0.598	0.918	1.56	2.57	2.74	13.5	8.00	13.5	3.25	0.598	0.103	0.488
15	0.532	1.20	1.68	2.40	2.91	12.0	10.5	9.00	3.08	0.598	0.084	0.488
16	0.824	1.20	1.68	1.80	2.40	9.00	8.50	7.67	2.57	0.532	0.065	0.652
17	0.730	1.20	1.92	1.80	2.40	8.25	7.00	7.00	2.40	0.466	0.084	0.652
18	0.730	1.20	1.80	2.16	2.91	8.00	6.00	6.00	2.16	0.466	0.065	0.652
19	1.01	1.44	2.16	1.92	4.48	8.75	5.62	5.43	1.92	0.466	0.065	0.816
20	1.44	2.57	2.04	2.16	6.00	8.75	5.62	5.05	1.80	0.330	0.065	0.816
21	1.44	4.10	2.16	1.92	8.25	9.00	5.81	4.86	1.68	0.275	0.065	1.14
22	1.32	2.91	2.16	2.04	9.50	8.50	5.62	4.67	1.92	0.220	0.065	2.37
23	1.32	2.28	2.16	2.04	9.00	9.50	5.24	4.48	1.68	0.220	0.065	1.31
24	1.20	2.28	2.04	1.80	8.75	15.2	5.05	4.10	1.56	0.488	0.084	0.012
25	1.20	3.08	1.68	1.92	10.5	13.0	4.67	3.93	1.32	6.93	0.084	0.010
26	1.32	4.48	1.56	1.80	15.8	9.00	4.29	3.93	1.20	5.22	0.065	0.015
27	1.20	4.48	1.56	1.80	13.5	8.00	3.93	3.93	1.11	4.65	0.103	0.013
28	1.20	4.29	1.68	1.80	10.0	7.67	3.76	3.76	1.11	4.65	0.084	0.816
29	1.44	3.59	2.04	1.56	-----	7.33	3.93	3.42	1.32	2.94	0.103	4.65
30	1.32	3.25	2.28	1.56	-----	8.00	4.29	3.08	1.68	2.94	0.084	5.22
31	1.32	-----	3.25	1.68	-----	9.00	-----	2.91	-----	2.37	0.103	-----
Maks.	3.08	5.62	5.05	5.24	20.0	23.9	14.0	17.6	8.00	22.2	3.51	6.36
Min.	0.532	0.918	1.44	1.44	1.56	7.00	3.76	2.57	1.01	0.147	0.052	0.010
Ortalama	0.967	2.01	2.13	2.53	4.92	9.72	6.61	6.11	2.30	1.56	0.426	0.969
LT/SN/Km2	1.09	2.27	2.40	2.86	5.56	11.0	7.46	6.90	2.59	1.76	0.481	1.09
AKIM mm.	2.92	5.87	6.43	7.65	13.5	29.4	19.3	18.5	6.72	4.71	1.29	2.84
MİL. M3	2.59	5.20	5.70	6.77	11.9	26.0	17.1	16.4	5.95	4.17	1.14	2.51

SU YILI (2006) YILLIK TOPLAM AKIM 105.43 MİLYON M3 119 MM. 3.8 LT/SN/Km2

13. Bati Karadeniz Havzasi

D13A062 ARAÇ Ç. KARIT

YERİ : **KARABÜK KASTAMONU KARAYOLUNUN 11.KM SİNDE ARAÇ ÇAYI ÜZERİNDEDIR.**
32°44'1" Doğu - 41°12'58" Kuzey

YAĞIŞ ALANI : **2571,40 km2** **YAKLAŞIK KOT : 362 m**

GÖZLEM SÜRESİ : **03.08.2000 - 30.09.2006**

ORTALAMA AKIMLAR : **Gözlem süresinde 11.242 m3/sn. (3 Yıllık) 2006 Su yılında 9.603 m3/sn.**

ANLIK EN ÇOK VE EN AZ AKIMLAR:

2006 Su yılında anlık ençok akım	:	**151.**	**m3/sn**	**04.03.2006**
2006 Su yılında anlık enaz akım	:	**0.837**	**m3/sn**	**10.09.2006**
Gözlem süresinde anlık ençok akım	:	**163.**	**m3/sn**	**28.02.2004**
Gözlem süresinde anlık enaz akım	:	**0.520**	**m3/sn**	**24.09.2004**

101. Anahtar Eğrisi (Seviyeler cm olarak)

Seviye	Akım	Seviye	Akım	Seviye	Akım	Seviye	Akım
64	0.145	148	20.7	234	109.	343	384.
80	1.2	165	31.2	251	140.	372	493.
97	3.4	182	45.2	271	180.	404	633.
114	7.2	200	62.7	293	232.	439	813.
131	12.8	216	83.0	317	299.		

Akımlar 01 Ekim 2005 'den 30 Eylül 2006' a kadar m3/sn olarak

Gün	Ekim	Kasım	Aralık	Ocak	Şubat	Mart	Nisan	Mayıs	Haziran	Temmuz	Ağustos	Eylül
01	3.14	3.32	7.92	13.0	5.60	69.4	19.4	9.00	4.38	2.78	1.22	1.06
02	2.96	3.32	7.20	12.2	5.40	70.8	18.0	11.4	4.38	2.96	1.30	1.14
03	3.14	3.32	6.56	10.6	5.20	72.2	17.5	11.8	4.16	2.96	1.40	1.06
04	3.72	3.32	6.56	9.40	5.20	90.4	16.5	11.0	3.94	2.60	1.40	0.980
05	3.14	3.32	6.24	9.00	5.20	56.0	15.5	9.80	3.72	2.28	1.30	0.980
06	2.96	3.50	6.56	11.4	5.40	45.6	15.0	9.40	3.50	2.12	1.06	0.980
07	2.78	3.50	6.24	16.0	5.92	41.6	14.5	9.80	3.32	1.80	1.14	0.980
08	2.60	3.72	5.60	20.8	6.24	42.4	15.0	16.0	3.50	1.80	1.22	0.980
09	2.44	3.72	5.40	16.5	6.56	46.4	16.5	14.0	4.38	1.80	1.30	0.900
10	2.44	3.50	5.20	14.0	6.56	37.9	16.0	13.0	5.60	1.60	1.14	0.900
11	2.44	3.50	5.00	12.2	9.40	37.2	17.5	12.2	5.60	1.60	1.06	1.06
12	2.44	3.32	4.80	11.0	14.5	37.9	17.0	11.4	5.60	1.60	1.14	0.980
13	2.60	3.14	4.80	10.2	13.0	38.6	16.5	12.2	5.20	1.50	1.14	0.980
14	2.60	3.14	4.60	9.40	11.8	40.0	15.5	20.1	5.20	1.50	1.14	1.06
15	2.60	3.50	4.60	8.64	11.0	37.9	16.0	16.0	5.60	1.50	1.14	1.14
16	2.60	3.94	4.60	8.28	10.2	33.7	16.0	13.5	5.00	1.40	1.14	1.06
17	2.60	3.94	4.80	7.56	9.40	29.8	14.0	12.2	4.60	1.40	1.14	1.06
18	2.60	3.72	5.00	7.20	10.6	28.2	12.6	11.4	4.16	1.40	1.06	1.14
19	2.60	3.50	5.20	7.20	24.3	28.2	11.8	10.2	3.50	1.70	1.06	1.14
20	4.38	3.94	5.60	7.20	39.3	27.4	11.4	9.00	3.32	1.60	1.06	1.22
21	5.00	7.20	5.60	6.88	41.6	26.6	11.0	8.64	2.96	1.50	0.980	1.22
22	4.80	8.64	5.20	6.56	46.4	25.0	11.0	7.92	2.96	1.50	1.14	1.22
23	3.94	7.20	5.20	6.56	44.8	23.6	10.6	7.56	2.96	1.60	1.06	1.30
24	3.50	6.24	5.20	6.24	43.2	30.6	10.2	6.88	2.78	1.60	0.980	1.30
25	3.14	7.20	5.20	5.92	42.4	31.4	9.80	6.56	2.60	1.60	0.980	1.30
26	3.14	11.0	5.00	5.92	65.0	26.6	9.00	5.92	2.44	1.50	0.980	1.30
27	2.96	11.4	5.00	5.92	86.8	22.9	8.64	6.24	2.28	1.40	0.980	1.30
28	2.96	11.0	5.00	5.60	69.4	20.8	8.28	5.92	2.60	1.40	0.980	1.40
29	2.96	9.40	6.56	5.40	-----	19.4	7.92	5.60	2.60	1.40	0.980	1.40
30	2.96	9.00	7.56	5.00	-----	18.7	8.28	5.20	2.78	1.30	0.980	1.50
31	3.14	-----	8.28	5.20	-----	20.8	-----	4.80	-----	1.30	0.980	-----
Maks.	5.92	12.6	9.80	22.9	98.8	151.	20.1	22.2	6.88	2.96	1.50	1.80
Min.	2.28	3.14	4.38	4.80	5.00	18.0	7.92	4.60	1.80	1.22	0.900	0.837
Ortalama	3.07	5.28	5.69	9.26	23.2	38.0	13.6	10.1	3.85	1.74	1.12	1.13
LT/SN/Km2	1.20	2.05	2.21	3.60	9.03	14.8	5.27	3.95	1.50	0.677	0.434	0.441
AKIM mm.	3.20	5.32	5.92	9.64	21.9	39.6	13.7	10.6	3.88	1.81	1.16	1.14
MİL. M3	8.23	13.7	15.2	24.8	56.2	102.	35.2	27.2	9.99	4.67	2.99	2.94

SU YILI (2006) YILLIK TOPLAM AKIM 303.12 MİLYON M3 118 MM. 3.7 LT/SN/Km2

13. Bati Karadeniz Havzasi

D13A063 SOĞANLI Ç. KARABÜK

YERİ : **KARABÜK GEREDE KARAYOLUNUN, KARABÜK ÇIKIŞINDAKİ KARAYOLU KÖPRÜSÜNE 500 M. MESAFEDE BULUNAN AŞAĞIKIZILÖREN KÖYÜ MERKEZİNDEDIR.**
32°38'30" Doğu - 41°10'9" Kuzey

YAĞIŞ ALANI : **5086,80 km2** **YAKLAŞIK KOT : 270 m**

GÖZLEM SÜRESİ : **04.08.2000 - 30.09.2006**

ORTALAMA AKIMLAR : **Gözlem süresinde 16.263 m3/sn. (3 Yıllık) 2006 Su yılında 13.694 m3/sn.**

ANLIK EN ÇOK VE EN AZ AKIMLAR:

2006 Su yılında anlık ençok akım	**:**	**82.0**	**m3/sn**	**26.03.2006**
2006 Su yılında anlık enaz akım	**:**	**1.40**	**m3/sn**	**11.09.2006**
Gözlem süresinde anlık ençok akım	**:**	**262.**	**m3/sn**	**29.02.2004**
Gözlem süresinde anlık enaz akım	**:**	**1.40**	**m3/sn**	**11.09.2006**

2011. Anahtar Eğrisi (Seviyeler cm olarak)

Seviye	Akım	Seviye	Akım	Seviye	Akım	Seviye	Akım
6	2.3	65	17.0	125	65.1	185	259.
17	4.2	77	22.5	137	85.6	197	346.
29	6.5	89	29.6	149	112.	210	467.
41	9.2	102	38.7	161	148.	221	622.
53	12.7	113	50.2	174	197.	233	833.

Akımlar 01 Ekim 2005 'den 30 Eylül 2006' a kadar m3/sn olarak

Gün	Ekim	Kasım	Aralık	Ocak	Şubat	Mart	Nisan	Mayıs	Haziran	Temmuz	Ağustos	Eylül
01	3.40	4.40	14.0	7.60	5.60	60.0	62.0	17.6	7.60	3.95	2.50	2.11
02	3.25	4.40	13.0	8.00	5.60	59.0	61.0	20.6	7.20	4.90	2.36	2.11
03	3.70	4.20	11.3	8.30	5.60	64.0	56.0	22.4	7.20	4.60	2.36	2.11
04	4.40	4.40	10.9	8.30	5.60	64.0	51.6	23.0	7.20	3.95	2.36	2.11
05	3.70	4.60	10.5	8.30	5.60	60.0	49.2	21.2	6.90	3.55	2.36	2.11
06	3.55	4.40	10.1	8.60	5.60	48.4	46.0	19.4	6.30	3.25	2.22	2.11
07	3.55	4.40	9.36	8.60	6.00	47.6	45.2	21.2	5.40	3.10	2.22	2.11
08	3.55	4.60	8.98	9.74	6.30	50.0	46.0	21.2	5.20	3.10	2.22	2.11
09	3.55	4.60	8.30	9.74	6.30	58.0	50.0	20.6	5.40	3.10	2.22	2.11
10	3.55	4.40	8.00	9.36	6.30	56.0	55.0	20.0	7.20	2.95	2.22	2.11
11	3.40	4.40	7.60	8.98	6.90	49.2	56.0	19.4	6.30	2.80	2.11	1.80
12	3.55	4.40	7.20	8.60	8.00	46.8	54.0	18.2	6.30	2.65	2.11	1.50
13	3.55	4.40	6.90	8.30	7.60	49.2	53.2	17.6	6.00	2.65	2.11	1.50
14	3.55	4.40	6.60	8.00	7.60	60.0	56.0	21.2	6.30	2.65	2.11	1.50
15	3.55	5.40	6.30	7.60	7.60	70.0	58.0	18.2	6.30	2.65	2.11	1.50
16	3.55	5.40	6.30	7.20	7.60	68.0	52.4	16.6	6.00	2.65	2.11	1.50
17	3.55	5.20	6.30	6.90	7.20	54.0	47.6	15.4	5.60	2.65	2.11	1.50
18	3.55	4.90	6.00	6.30	7.60	48.4	42.8	15.0	5.20	2.36	2.11	1.40
19	3.55	4.90	6.30	6.30	9.36	44.4	38.0	14.0	4.90	2.22	2.11	1.50
20	5.80	5.40	6.90	6.60	10.9	39.0	35.2	13.0	4.40	2.22	2.11	1.50
21	5.60	8.60	6.60	6.60	12.1	36.4	33.2	12.5	3.95	2.11	2.11	1.50
22	4.90	8.00	6.30	6.30	15.4	34.0	32.4	11.7	4.40	2.11	2.11	2.22
23	4.40	8.30	6.60	6.30	19.4	34.6	30.0	10.9	4.40	2.11	2.11	2.95
24	4.40	8.00	6.30	6.30	23.8	50.0	28.2	10.5	3.95	5.60	2.11	2.50
25	4.40	7.60	6.30	6.30	28.8	75.0	27.0	9.74	3.55	3.55	2.11	2.65
26	4.40	8.00	6.60	6.30	34.6	77.0	24.6	9.74	3.40	2.95	2.11	2.80
27	4.20	9.36	6.60	6.00	50.0	64.0	21.8	9.74	4.20	2.80	2.11	2.50
28	3.95	12.5	6.60	6.00	61.0	59.0	19.4	9.36	3.95	2.65	2.11	2.50
29	4.20	15.0	6.60	5.80	-----	54.0	18.2	8.98	3.70	2.50	2.11	2.50
30	4.40	15.8	6.60	5.60	-----	53.2	17.0	8.30	3.55	2.50	2.11	2.65
31	4.40	-----	6.60	5.60	-----	57.0	-----	8.00	-----	2.50	2.11	-----
Maks.	6.60	16.6	15.0	9.74	67.0	82.0	66.0	23.8	12.5	11.3	2.50	4.20
Min.	3.25	4.20	5.80	5.20	5.20	32.4	16.6	8.00	3.25	2.00	2.00	1.40
Ortalama	3.97	6.48	7.82	7.37	13.7	54.5	42.2	15.7	5.40	3.01	2.17	2.04
LT/SN/Km2	0.780	1.27	1.54	1.45	2.70	10.7	8.30	3.08	1.06	0.592	0.427	0.400
AKIM mm.	2.09	3.30	4.12	3.88	6.52	28.7	21.5	8.24	2.75	1.59	1.14	1.04
MİL. M3	10.6	16.8	21.0	19.7	33.2	146.	109.	41.9	14.0	8.06	5.82	5.28

SU YILI (2006) YILLIK TOPLAM AKIM 431.36 MİLYON M3 85 MM. 2.7 LT/SN/Km2

13. Bati Karadeniz Havzasi

D13A064 GEREDE ÇAYI BAYRAMÖREN

YERİ : **BAYRAMÖREN OYMAAĞAÇ KÖY YOLUNUN 1,5 KM SİNDEKİ KÖPRÜNÜN ÜZERİNDEDİR.**
33°13'33" Doğu - 40°57'24" Kuzey

YAĞIŞ ALANI : **3002.00 km2** **YAKLAŞIK KOT : 745 m**

GÖZLEM SÜRESİ : **31.07.2002 - 30.09.2006**

ORTALAMA AKIMLAR : **Gözlem süresinde 15.153 m3/sn. (3 Yıllık) 2006 Su yılında 12.067 m3/sn.**

ANLIK EN ÇOK VE EN AZ AKIMLAR:

2006 Su yılında anlık ençok akım	**:**	**96.5**	**m3/sn**	**26.03.2006**
2006 Su yılında anlık enaz akım	**:**	**0.890**	**m3/sn**	**03.08.2006**
Gözlem süresinde anlık ençok akım	**:**	**338.**	**m3/sn**	**29.02.2004**
Gözlem süresinde anlık enaz akım	**:**	**0.770**	**m3/sn**	**24.09.2005**

İstasyon için kullanılmış anahtar bulunamadı.

Akımlar 01 Ekim 2005 'den 30 Eylül 2006' a kadar m3/sn olarak

Gün	Ekim	Kasım	Aralık	Ocak	Şubat	Mart	Nisan	Mayıs	Haziran	Temmuz	Ağustos	Eylül
01	2.15	2.57	9.16	5.78	13.9	46.0	45.0	13.3	4.50	1.95	1.01	0.890
02	2.15	2.57	8.32	5.78	13.9	48.0	51.0	15.6	3.98	1.95	1.01	0.890
03	2.15	2.57	7.90	5.78	13.9	62.0	46.0	18.5	3.98	1.95	0.890	1.01
04	2.15	2.57	7.90	5.78	13.3	58.7	43.0	17.2	3.98	1.95	0.890	1.01
05	2.15	2.57	7.90	5.78	13.3	55.4	39.3	15.6	4.24	1.95	0.890	0.890
06	2.15	2.57	8.32	5.78	13.3	53.2	35.1	14.4	4.50	1.75	0.890	0.890
07	2.15	2.57	8.32	5.78	13.9	51.0	32.5	13.9	4.50	1.75	0.890	0.890
08	2.15	2.57	8.32	5.46	13.9	50.0	32.5	13.9	4.50	1.75	0.890	0.890
09	2.15	2.78	7.90	5.46	14.4	50.0	33.4	14.4	4.24	1.75	0.890	0.890
10	2.15	2.99	7.54	5.46	14.4	49.0	39.3	13.9	3.98	1.75	0.890	0.890
11	2.15	2.99	7.54	7.90	14.4	50.0	45.0	13.3	3.98	1.75	0.890	0.890
12	2.15	2.99	6.82	7.18	14.4	49.0	43.0	12.2	3.98	1.60	1.01	0.890
13	2.15	2.99	6.82	7.18	14.4	51.0	45.0	12.2	3.72	1.60	1.01	0.890
14	2.15	3.20	6.46	6.46	14.4	68.5	50.0	11.3	3.72	1.60	1.01	0.890
15	2.15	3.20	6.46	7.90	14.4	56.5	47.0	11.3	3.46	1.60	1.01	0.890
16	2.15	3.46	6.10	7.54	14.4	51.0	42.0	10.0	3.46	1.60	1.13	0.890
17	2.15	3.46	5.46	7.18	15.6	50.0	37.6	10.0	3.20	1.60	1.13	0.890
18	2.15	3.46	5.46	7.18	21.2	49.0	31.7	9.16	3.20	1.43	1.01	0.890
19	2.15	3.46	5.46	7.90	19.8	51.0	28.5	9.16	2.99	1.43	1.01	1.43
20	2.15	3.72	6.10	7.90	19.1	52.1	26.1	8.74	2.78	1.43	1.01	1.29
21	2.36	7.18	6.10	7.90	19.1	56.5	25.3	8.32	2.78	1.29	0.890	1.29
22	2.57	6.46	5.78	8.32	17.8	62.0	24.5	7.90	2.78	1.29	0.890	1.29
23	2.57	6.10	5.46	8.32	19.8	56.5	22.5	7.90	2.57	1.29	0.890	1.29
24	2.57	5.78	5.14	7.90	20.5	51.0	21.2	7.18	2.57	1.29	0.890	1.29
25	2.57	5.46	5.14	8.32	24.5	62.0	19.8	6.82	2.57	1.29	0.890	1.43
26	2.57	5.46	5.14	11.3	51.0	71.1	17.8	6.82	2.36	1.29	0.890	1.43
27	2.57	5.46	5.14	13.3	56.5	64.6	15.6	6.10	2.15	1.13	1.01	1.43
28	2.57	6.10	5.46	12.2	51.0	56.5	13.9	5.78	2.15	1.13	1.01	1.43
29	2.57	10.0	5.46	12.2	-----	51.0	12.2	5.78	2.15	1.13	1.01	1.43
30	2.57	9.16	5.78	15.0	-----	46.0	11.8	5.46	1.95	1.13	1.01	1.43
31	2.57	-----	5.78	13.9	-----	44.0	-----	4.82	-----	1.13	1.01	-----
Maks.	2.99	12.2	9.58	19.8	68.5	96.5	56.5	21.2	4.82	1.95	1.75	3.98
Min.	1.95	2.36	4.82	5.46	13.3	41.0	11.3	4.50	1.75	1.13	0.890	0.890
Ortalama	2.29	4.21	6.60	8.06	20.0	54.0	32.6	10.7	3.36	1.53	0.960	1.09
LT/SN/Km2	0.764	1.40	2.20	2.68	6.67	18.0	10.9	3.56	1.12	0.511	0.320	0.363
AKIM mm.	2.05	3.64	5.89	7.19	16.1	48.1	28.1	9.52	2.90	1.37	0.856	0.942
MİL. M3	6.14	10.9	17.7	21.6	48.4	145.	84.5	28.6	8.72	4.11	2.57	2.83

SU YILI (2006) YILLIK TOPLAM AKIM 381.07 MİLYON M3 127 MM. 4.0 LT/SN/Km2

13. Bati Karadeniz Havzasi

D13A065 BÜYÜKSU ÇAYI KÜPLÜCE KÖPRÜSÜ

YERİ : **BOLU ÇİMENTO FABRİKASININ (E-5 KARAYOLU)-GÖKÇESU YOLUNUN 18.KM SİNDE KÜPLÜCE YOLU ÜZERİNDEKİ KÖPRÜDEDİR.**
31°51'60" Doğu - 40°51'48" Kuzey

YAĞIŞ ALANI : **1053.00 km2** **YAKLAŞIK KOT : 613 m**

GÖZLEM SÜRESİ : **31.07.2002 – 30.09.2006**

ORTALAMA AKIMLAR : **Gözlem süresinde 7.197 m3/sn. (3 Yıllık) 2006 Su yılında 6.209 m3/sn.**

ANLIK EN ÇOK VE EN AZ AKIMLAR:

2006 Su yılında anlık ençok akım	**:**	**53.8**	**m3/sn**	**03.03.2006**
2006 Su yılında anlık enaz akım	**:**	**1.10**	**m3/sn**	**29.08.2006**
Gözlem süresinde anlık ençok akım	**:**	**99.0**	**m3/sn**	**28.02.2004**
Gözlem süresinde anlık enaz akım	**:**	**1.10**	**m3/sn**	**29.08.2006**

İstasyon için kullanılmış anahtar bulunamadı.

Akımlar 01 Ekim 2005 'den 30 Eylül 2006' a kadar m3/sn olarak

Gün	Ekim	Kasım	Aralık	Ocak	Şubat	Mart	Nisan	Mayıs	Haziran	Temmuz	Ağustos	Eylül
01	2.68	3.74	5.24	8.19	4.45	25.1	11.5	7.99	2.68	2.81	1.64	2.42
02	2.94	2.68	4.75	6.65	4.30	33.2	11.0	7.60	2.68	3.61	1.77	1.52
03	3.07	2.68	4.60	6.47	4.30	30.9	10.8	7.41	2.68	3.88	2.03	1.30
04	2.94	2.68	4.60	6.47	4.60	22.7	10.3	7.60	2.68	2.94	1.90	1.30
05	2.68	3.47	4.75	7.80	4.75	20.1	10.0	8.19	2.81	2.94	1.64	1.20
06	7.03	4.90	4.45	7.22	5.07	20.1	9.55	8.19	2.81	3.07	1.77	1.20
07	5.75	4.75	4.15	6.65	5.07	24.3	10.3	9.16	3.34	2.81	1.90	1.20
08	3.47	3.88	3.74	6.11	4.90	23.9	10.8	9.16	3.47	2.81	1.90	1.10
09	3.61	3.34	3.74	5.58	4.60	19.8	10.5	7.99	3.88	2.68	1.77	1.10
10	3.34	3.34	3.74	5.41	11.5	19.4	10.0	7.41	3.74	2.55	2.03	1.20
11	3.61	3.07	3.61	5.41	10.8	25.1	8.38	9.36	4.90	2.29	1.77	1.30
12	3.34	3.07	3.47	5.24	8.38	29.6	7.99	9.36	4.75	2.03	1.90	1.20
13	3.47	3.07	3.34	5.07	6.11	26.4	8.19	7.80	4.30	2.16	1.90	1.20
14	3.34	3.47	3.61	4.90	5.93	23.5	7.99	6.11	3.47	2.42	2.03	1.20
15	3.61	3.34	3.74	4.45	5.41	19.1	7.80	6.11	3.47	2.29	1.90	1.20
16	3.47	3.21	4.01	4.60	5.75	15.0	7.80	5.58	3.34	2.42	2.03	1.10
17	3.34	3.34	3.61	4.60	6.65	14.4	7.80	5.41	3.34	2.68	2.03	1.20
18	3.34	3.47	3.88	5.07	11.8	14.4	7.60	5.24	3.34	2.42	1.64	1.41
19	3.61	3.34	4.01	4.90	18.7	13.2	7.60	5.24	3.47	2.55	1.41	1.64
20	4.15	3.88	3.34	4.75	22.3	12.9	7.60	4.75	3.21	2.81	1.30	1.77
21	10.8	6.29	3.21	4.60	21.5	12.0	6.84	4.60	2.81	2.68	1.30	2.29
22	5.93	4.45	3.74	4.90	21.9	13.8	6.29	3.88	2.68	2.55	1.20	1.90
23	4.01	4.45	3.88	4.60	21.9	18.7	6.29	3.61	2.68	2.29	1.30	1.90
24	4.01	8.19	3.74	4.60	21.9	18.7	6.11	3.61	2.68	2.16	1.30	2.55
25	3.61	14.7	3.88	4.60	32.3	15.9	6.47	3.61	2.55	2.29	1.20	2.03
26	3.34	19.1	3.88	4.60	34.5	14.7	6.65	3.47	2.94	2.03	1.20	1.77
27	3.34	16.2	4.75	4.30	27.3	14.1	6.65	3.47	3.74	2.16	1.30	1.77
28	3.61	13.8	7.41	3.74	26.0	13.8	6.65	3.74	3.47	1.90	1.30	2.29
29	3.88	8.58	8.38	3.74	-----	13.5	6.47	3.61	3.21	1.77	1.10	3.21
30	4.01	8.97	8.38	4.15	-----	12.0	6.84	3.07	2.94	1.64	1.10	2.81
31	3.88	-----	10.5	4.45	-----	12.0	-----	2.81	-----	1.64	1.64	-----
Maks.	13.5	25.1	11.3	13.2	45.8	53.8	13.2	13.5	5.93	5.24	2.94	4.45
Min.	2.68	2.68	3.21	3.74	4.30	12.0	6.11	2.81	2.55	1.64	1.10	1.10
Ortalama	3.97	5.78	4.58	5.28	13.0	19.1	8.29	5.97	3.27	2.49	1.62	1.64
LT/SN/Km2	3.77	5.49	4.35	5.02	12.3	18.1	7.87	5.67	3.10	2.37	1.54	1.56
AKIM mm.	10.1	14.2	11.7	13.4	29.8	48.6	20.4	15.2	8.05	6.34	4.12	4.04
MİL. M3	10.6	15.0	12.3	14.2	31.3	51.2	21.5	16.0	8.47	6.68	4.34	4.26

SU YILI (2006) YILLIK TOPLAM AKIM 195.85 MİLYON M3 186 MM. 5.9 LT/SN/Km2

13. Bati Karadeniz Havzasi

D13A068 ABANT DERESİ AKÇAALAN

YERİ : **E5-ABANT YOLUNUN 5.KM SİNDE AKÇAALAN KÖYÜ GİRİŞİNDEDİR.**
31°26'23" Doğu - 40°40'31" Kuzey

YAĞIŞ ALANI : **86.50 km2** **YAKLAŞIK KOT : 855 m**

GÖZLEM SÜRESİ : **31.07.2002 - 30.09.2006**

ORTALAMA AKIMLAR : **Gözlem süresinde 1.220 m3/sn. (2 Yıllık) 2006 Su yılında 1.012 m3/sn.**

ANLIK EN ÇOK VE EN AZ AKIMLAR:

2006 Su yılında anlık ençok akım	:	**6.87**	**m3/sn**	**24.03.2006**
2006 Su yılında anlık enaz akım	:	**0.122**	**m3/sn**	**25.08.2006**
Gözlem süresinde anlık ençok akım	:	**7.30**	**m3/sn**	**03.03.2005**
Gözlem süresinde anlık enaz akım	:	**0.122**	**m3/sn**	**25.08.2006**

İstasyon için kullanılmış anahtar bulunamadı.

Akımlar 01 Ekim 2005 'den 30 Eylül 2006' a kadar m3/sn olarak

Gün	Ekim	Kasım	Aralık	Ocak	Şubat	Mart	Nisan	Mayıs	Haziran	Temmuz	Ağustos	Eylül
01	0.255	0.545	1.28	1.28	0.870	3.16	3.02	1.18	0.583	0.469	0.190	0.469
02	0.255	0.495	1.13	1.07	0.870	2.88	2.88	1.18	0.583	0.412	0.190	0.412
03	0.255	0.495	1.13	1.07	0.870	4.65	2.88	1.09	0.583	0.640	0.190	0.355
04	0.255	0.450	1.13	1.07	0.870	3.60	2.74	1.09	0.526	0.526	0.190	0.355
05	0.255	0.450	1.20	1.28	0.646	2.88	2.60	1.09	0.526	0.469	0.190	0.355
06	0.290	0.545	1.07	1.36	0.646	2.74	2.48	1.09	0.583	0.469	0.190	0.355
07	0.290	0.936	1.00	1.28	0.758	3.02	2.60	1.09	0.583	0.412	0.190	0.355
08	0.290	0.814	0.936	1.13	0.758	3.75	2.74	1.09	0.583	0.412	0.190	0.355
09	0.290	0.646	0.936	1.07	0.758	3.16	2.60	1.18	0.583	0.412	0.190	0.355
10	0.290	0.590	0.936	1.00	0.814	2.74	2.36	1.09	0.583	0.412	0.190	0.355
11	0.255	0.590	0.870	0.936	1.52	2.48	2.36	1.00	0.583	0.412	0.190	0.355
12	0.255	0.545	0.870	0.870	1.36	3.60	2.48	1.00	0.583	0.355	0.190	0.355
13	0.255	0.495	0.814	0.870	1.13	4.20	2.48	1.56	0.640	0.355	0.190	0.355
14	0.255	0.590	0.758	0.870	1.00	4.05	2.24	1.27	0.640	0.355	0.190	0.355
15	0.255	0.590	0.758	0.814	1.00	3.60	2.12	1.09	0.583	0.355	0.190	0.355
16	0.255	0.545	0.814	0.814	0.870	3.16	2.00	1.00	0.526	0.355	0.190	0.355
17	0.255	0.495	0.814	0.936	0.870	2.88	1.78	0.928	0.526	0.355	0.190	0.355
18	0.255	0.870	0.758	0.758	1.00	2.60	1.67	0.928	0.469	0.355	0.190	0.190
19	0.290	0.758	0.870	0.758	1.20	2.48	1.56	0.856	0.469	0.305	0.190	0.154
20	0.870	1.96	0.870	0.758	1.52	2.36	1.56	0.856	0.469	0.305	0.190	0.190
21	0.758	1.28	0.814	0.758	1.60	2.36	1.45	0.856	0.469	0.305	0.190	0.190
22	0.646	1.00	0.814	0.758	1.69	2.48	1.45	0.856	0.412	0.305	0.190	0.190
23	0.646	0.814	0.814	0.758	1.87	3.45	1.36	0.784	0.412	0.305	0.154	0.190
24	0.590	1.28	0.814	0.814	1.96	4.35	1.36	0.712	0.412	0.305	0.154	0.190
25	0.590	2.05	0.758	0.814	2.49	3.60	1.36	0.712	0.412	0.265	0.122	0.305
26	0.545	2.88	0.870	0.870	3.45	3.02	1.27	0.712	0.412	0.265	0.122	0.225
27	0.495	2.74	1.00	0.870	3.16	2.88	1.27	0.712	0.412	0.265	0.122	0.190
28	0.450	2.27	1.13	0.870	2.88	2.88	1.18	0.712	0.412	0.225	0.122	0.190
29	0.646	1.87	1.07	0.870	-----	2.88	1.27	0.640	0.469	0.225	0.122	0.265
30	0.545	1.52	1.00	0.870	-----	3.16	1.18	0.640	0.469	0.225	0.122	0.412
31	0.545	-----	1.36	0.870	-----	3.02	-----	0.583	-----	0.225	0.122	-----
Maks.	1.36	3.90	1.78	1.60	4.35	6.87	3.30	2.74	0.856	1.18	0.225	1.67
Min.	0.255	0.450	0.758	0.702	0.646	2.12	1.18	0.583	0.412	0.190	0.122	0.122
Ortalama	0.399	1.04	0.948	0.939	1.37	3.16	2.01	0.954	0.517	0.357	0.172	0.303
LT/SN/Km2	4.62	12.0	11.0	10.9	15.9	36.6	23.2	11.0	5.97	4.12	1.99	3.50
AKIM mm.	12.4	31.1	29.4	29.1	38.4	98.0	60.2	29.5	15.5	11.0	5.34	9.08
MİL. M3	1.07	2.69	2.54	2.52	3.32	8.47	5.21	2.56	1.34	0.955	0.462	0.785

SU YILI (2006) YILLIK TOPLAM AKIM 31.92 MİLYON M3 369 MM. 11.7 LT/SN/Km2

13. Bati Karadeniz Havzasi

D13A070 HIZAR DERESİ BAYRAMIŞLAR KÖPRÜSÜ

YERİ : **BOLU - YEDİGÖLLER YOLU 10.KM SİNDE BAYRAMIŞLAR KÖPRÜSÜNDEDİR.**
31°38'5" Doğu - 40°47'23" Kuzey

YAĞIŞ ALANI : **24.45 km2** **YAKLAŞIK KOT : 900 m**

GÖZLEM SÜRESİ : **01.10.2005 - 30.09.2006**

ORTALAMA AKIMLAR : **Gözlem süresinde 0.228 m3/sn. (1 Yıllık) 2006 Su yılında 0.228 m3/sn.**

ANLIK EN ÇOK VE EN AZ AKIMLAR:

2006 Su yılında anlık ençok akım	**:**	**2.60**	**m3/sn**	**25.02.2006**
2006 Su yılında anlık enaz akım	**:**	**0.024**	**m3/sn**	**02.07.2006**
Gözlem süresinde anlık ençok akım	**:**	**2.60**	**m3/sn**	**25.02.2006**
Gözlem süresinde anlık enaz akım	**:**	**0.024**	**m3/sn**	**02.07.2006**

İstasyon için kullanılmış anahtar bulunamadı.

Akımlar 01 Ekim 2005 'den 30 Eylül 2006' a kadar m3/sn olarak

Gün	Ekim	Kasım	Aralık	Ocak	Şubat	Mart	Nisan	Mayıs	Haziran	Temmuz	Ağustos	Eylül
01	0.059	0.200	0.315	0.600	0.250	0.914	0.315	0.315	0.115	0.038	0.024	0.059
02	0.059	0.200	0.315	0.450	0.250	0.802	0.315	0.315	0.084	0.038	0.038	0.084
03	0.084	0.200	0.315	0.450	0.250	1.03	0.315	0.315	0.084	0.115	0.024	0.059
04	0.084	0.200	0.315	0.450	0.250	1.03	0.315	0.315	0.084	0.115	0.038	0.059
05	0.084	0.200	0.315	0.450	0.250	0.802	0.315	0.250	0.084	0.115	0.038	0.059
06	0.084	0.200	0.250	0.450	0.250	0.690	0.315	0.250	0.084	0.084	0.024	0.038
07	0.084	0.155	0.250	0.450	0.250	0.600	0.315	0.250	0.084	0.084	0.024	0.024
08	0.084	0.155	0.250	0.375	0.250	0.600	0.315	0.250	0.084	0.084	0.038	0.024
09	0.084	0.155	0.200	0.315	0.250	0.520	0.315	0.315	0.084	0.084	0.038	0.024
10	0.084	0.155	0.200	0.315	0.200	0.520	0.315	0.315	0.084	0.059	0.038	0.038
11	0.084	0.155	0.200	0.250	0.315	0.520	0.315	0.200	0.200	0.059	0.038	0.038
12	0.084	0.155	0.200	0.250	0.315	0.520	0.315	0.155	0.155	0.038	0.038	0.038
13	0.115	0.155	0.200	0.250	0.250	0.520	0.250	0.250	0.115	0.038	0.038	0.038
14	0.115	0.155	0.200	0.250	0.315	0.520	0.250	0.200	0.115	0.024	0.038	0.038
15	0.115	0.155	0.200	0.250	0.250	0.450	0.250	0.200	0.115	0.038	0.038	0.038
16	0.115	0.155	0.200	0.250	0.200	0.450	0.250	0.200	0.115	0.038	0.038	0.038
17	0.115	0.155	0.200	0.250	0.250	0.450	0.250	0.200	0.115	0.038	0.024	0.038
18	0.115	0.155	0.200	0.250	0.315	0.375	0.250	0.200	0.115	0.038	0.024	0.038
19	0.115	0.155	0.200	0.200	0.914	0.375	0.250	0.200	0.115	0.038	0.024	0.059
20	0.450	0.155	0.200	0.200	1.25	0.375	0.250	0.155	0.115	0.038	0.024	0.115
21	0.200	0.155	0.200	0.200	1.14	0.375	0.200	0.155	0.084	0.038	0.024	0.059
22	0.155	0.155	0.200	0.200	1.03	0.315	0.200	0.155	0.084	0.038	0.024	0.084
23	0.155	0.155	0.200	0.200	1.03	0.375	0.200	0.155	0.084	0.038	0.024	0.084
24	0.200	0.450	0.200	0.200	0.914	0.450	0.200	0.155	0.084	0.038	0.038	0.115
25	0.155	0.600	0.200	0.200	1.14	0.450	0.200	0.155	0.059	0.038	0.038	0.115
26	0.155	0.802	0.200	0.200	1.40	0.375	0.200	0.155	0.059	0.038	0.038	0.115
27	0.155	1.03	0.200	0.200	1.25	0.375	0.200	0.155	0.059	0.038	0.038	0.084
28	0.155	0.690	0.315	0.200	0.914	0.375	0.200	0.155	0.084	0.038	0.038	0.084
29	0.155	0.520	0.520	0.200	-----	0.375	0.200	0.155	0.038	0.038	0.038	0.115
30	0.155	0.375	0.520	0.250	-----	0.375	0.250	0.115	0.038	0.038	0.038	0.115
31	0.155	-----	0.690	0.250	-----	0.375	-----	0.115	-----	0.038	0.024	-----
Maks.	0.690	1.85	1.40	0.802	2.60	2.00	0.450	0.450	1.03	1.40	0.038	0.802
Min.	0.059	0.115	0.200	0.200	0.155	0.315	0.155	0.115	0.038	0.024	0.024	0.024
Ortalama	0.129	0.277	0.264	0.290	0.559	0.525	0.261	0.209	0.094	0.052	0.033	0.064
LT/SN/Km2	5.29	11.3	10.8	11.9	22.8	21.5	10.7	8.54	3.84	2.14	1.33	2.61
AKIM mm.	14.2	29.3	28.9	31.8	55.3	57.5	27.7	22.9	9.96	5.73	3.57	6.77
MİL. M3	0.346	0.717	0.706	0.778	1.35	1.41	0.677	0.559	0.244	0.140	0.087	0.166

SU YILI (2006) YILLIK TOPLAM AKIM 7.18 MİLYON M3 294 MM. 9.3 LT/SN/Km2

14

YEŞİLIRMAK HAVZASI

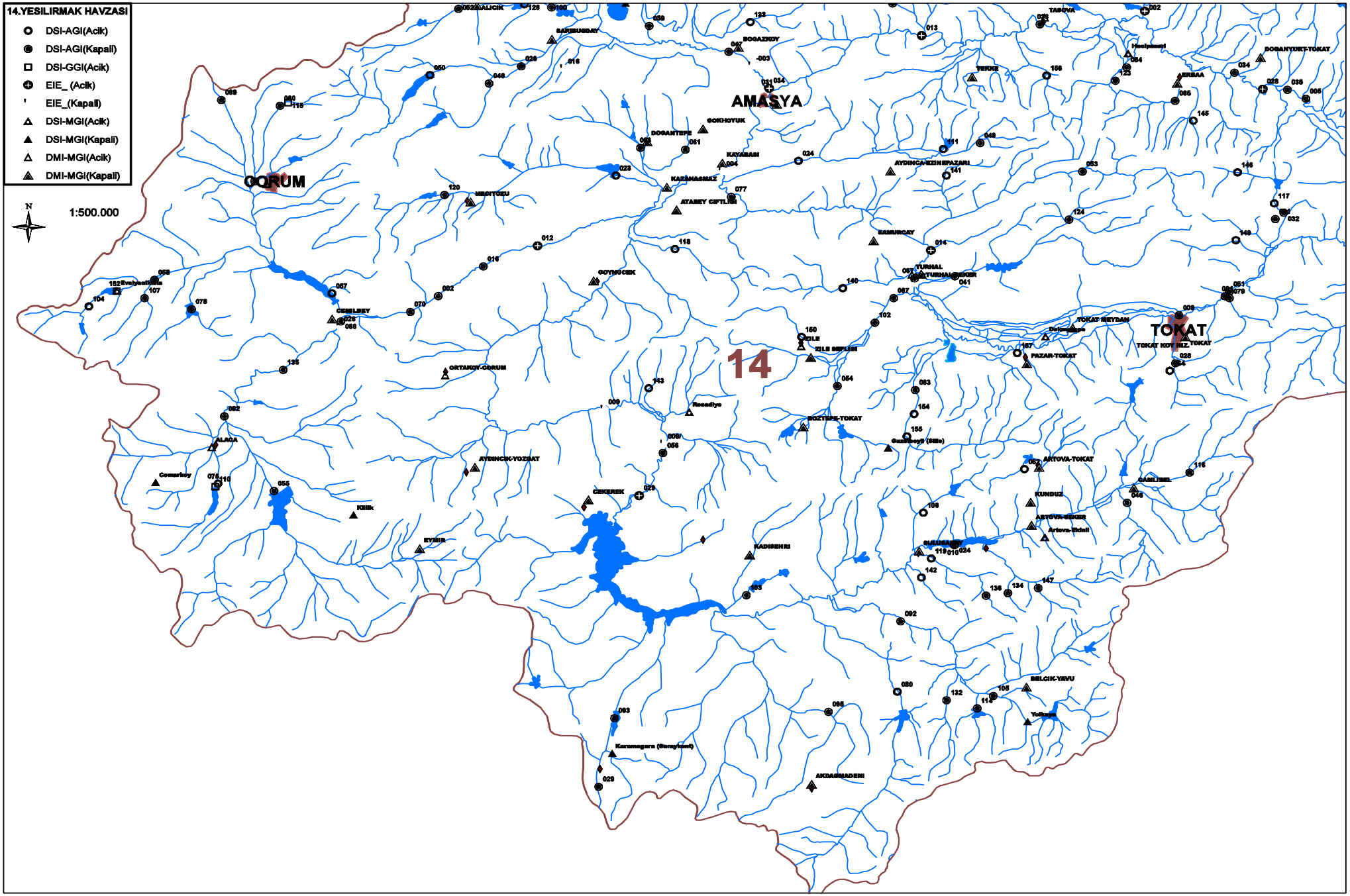
14.YESILIRMAK HAVZASI
DSI-AGI(Acik)
DSI-AGI(Kapali)
DSI-GGI(Acik)
EIE_ (Acik)
EIE_(Kapali)
DSI-MGI(Acik)
DSI-MGI(Kapali)
DMI-MGI(Acik)
DMI-MGI(Kapali)
N
1:500.000
AMASYA
ÇORUM
TOKAT
14
ALICIK
BARBUNDAY
BOGAZKOY
TASOVA
TEPEKÖY
ARMAA
DOGANYUKT-TOKAT
GÖKHOYUK
DOGANTEPE
KAYABASI
KAZANASMAZ
ATABEY ÇIFTLIGI
AYDINCA-KIZINIPAZARI
KAMURCAY
TURHAL
TURHAL-SEKER
ÇEMILBEY
GÖYNÜCEK
ÖZLE
ÖZLE SEFLIGI
TOKAT SEYDAN
TOKAT KOY HIZ.
PAZAR-TOKAT
ORTAKÖY-ÇORUM
Resadiye
BOZTEPE-TOKAT
Gaziköy (Sille)
ALACA
Comarköy
AYDINCIK-YOZGAT
AKTOVA-TOKAT
KUNDUZ
ÇAMLIBEL
AKTOVA-SEKER
Artova-Ekinli
ÇEKEREK
Kilik
EYMIR
KADISEHRI
SULUSARAY
BELCIK-YAVU
Yeliçay
Karamagara (Sarayönü)
AKDAGMADENI

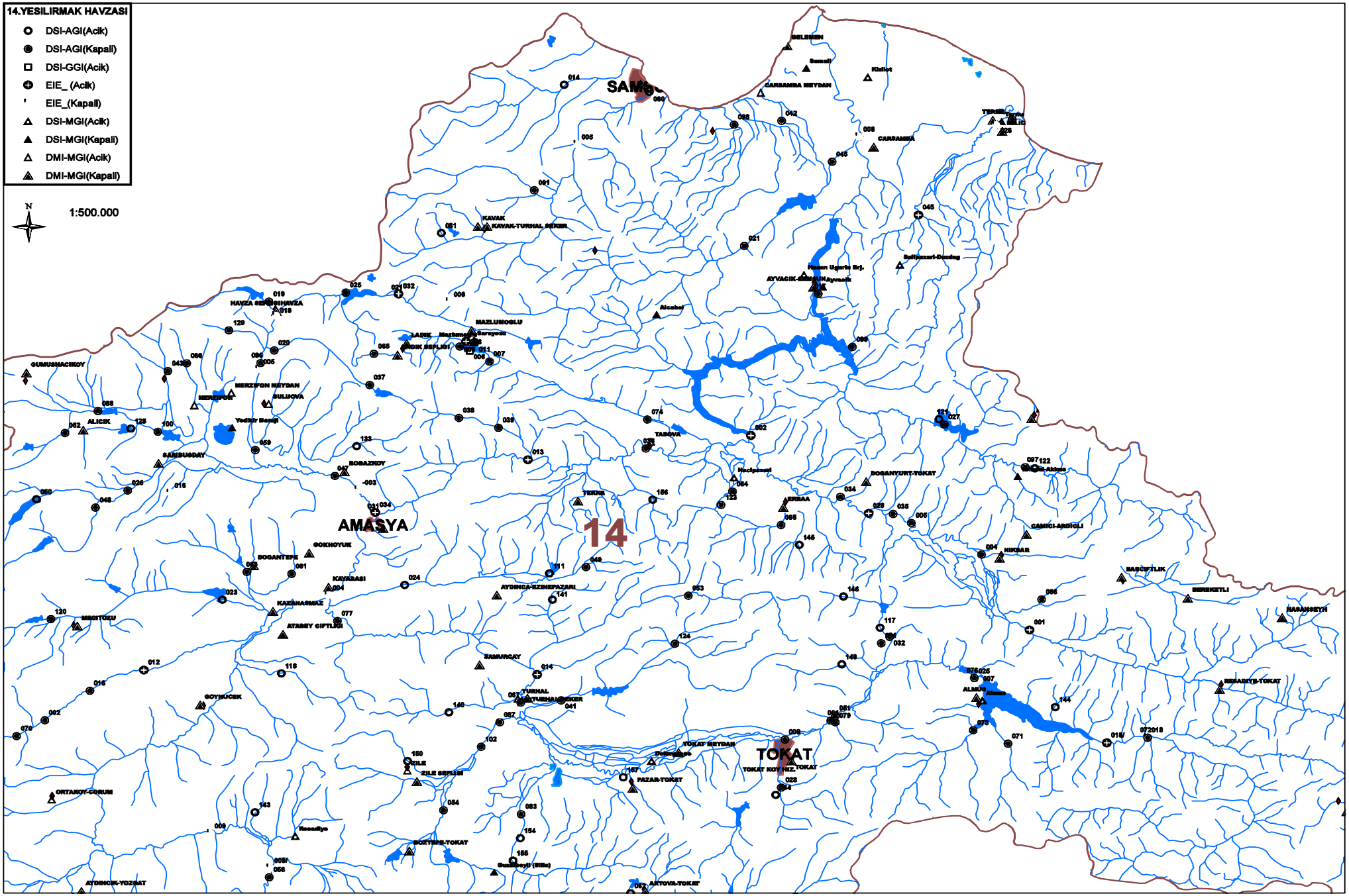
14.YESILIRMAK HAVZASI
DSI-AGI(Acik)
DSI-AGI(Kapali)
DSI-GGI(Acik)
EIE_ (Acik)
EIE_(Kapali)
DSI-MGI(Acik)
DSI-MGI(Kapali)
DMI-MGI(Acik)
DMI-MGI(Kapali)
N
1:500.000
SAMSUN
AMASYA
TOKAT
14
SILEHEN
Semali
Kizlot
CARSAMBA MEYDAN
CARSAMBA
TERME
KAVAK
KAVAK-TURMAL SEKER
HAVZA SEKERIHAVZA
MAZLUMOGLU
LADIK
LADIK SEFLIGI
GUMUSHACIKOY
MERZIFON MEYDAN
MERZIFON
BULUCOA
ALICIK
Yedikir Barajı
SARIBUGDAY
BOGAZKOY
TASOVA
Hacipasal
DOGANYURT-TOKAT
ERBAA
TEKKE
CAMICI-ARDICLI
NIKSAR
BASCIFTLIK
BERBERETLI
HASANBEYLI
DOGANTEPE
GOKNOYUK
KAYABASI
KAZANASMAZ
ATABEY CIFTLIGI
AYDINCA-EZINEPAZARI
MECITOZU
SAMURCAY
TURMAL
TURMAL SEKER
GOYNUCEK
ZILE
ZILE SEFLIGI
TOKAT MEYDAN
TOKAT KOY HIZ.-TOKAT
PAZAR-TOKAT
ALMUS
REDADIYE-TOKAT
OKTANCY-CORUM
Readiye
DOKTEPE-TOKAT
AYDINCIK-YOZGAT
ARTOVA-TOKAT

14.YESILIRMAK HAVZASI

- DSI-AGI(Acik)
- DSI-AGI(Kapali)
- DSI-GGI(Acik)
- EIE_ (Acik)
- EIE_(Kapali)
- DSI-MGI(Acik)
- DSI-MGI(Kapali)
- DMI-MGI(Acik)
- DMI-MGI(Kapali)

N

1:500.000

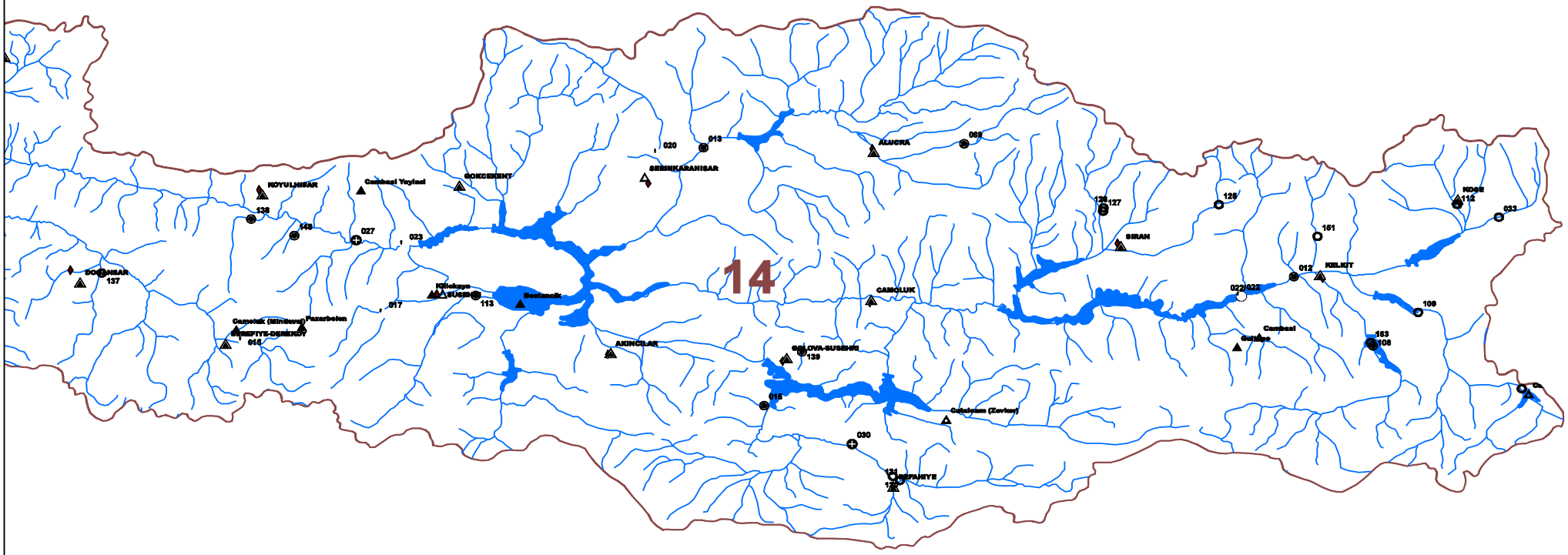

14. Yesilırmak Havzasi

D14A014 KÜRTÜN D. AHULLU

YERİ : **SAMSUN-ANKARA KARAYOLUNUN 11 KM SİNDEKİ ÇAĞLAYAN MEVKİİNDEDİR. 25 LİK PAFTAKİ YERİ F36-A3**
36°11'43" Doğu - 41°17'10" Kuzey

YAĞIŞ ALANI : **259,00 km2** **YAKLAŞIK KOT : 140 m**

GÖZLEM SÜRESİ : **01.10.1963 - 30.09.2006**

ORTALAMA AKIMLAR : **Gözlem süresinde 1.448 m3/sn. (42 Yıllık) 2006 Su yılında 1.190 m3/sn.**

ANLIK EN ÇOK VE EN AZ AKIMLAR:

2006 Su yılında anlık ençok akım	**:**	**19.5**	**m3/sn**	**27.03.2006**
2006 Su yılında anlık enaz akım	**:**	**0.190**	**m3/sn**	**06.10.2005**
Gözlem süresinde anlık ençok akım	**:**	**330.**	**m3/sn**	**21.05.1974**
Gözlem süresinde anlık enaz akım	**:**	**0.000**	**m3/sn**	**01.11.1992**

5. Anahtar Eğrisi (Seviyeler cm olarak)

Seviye	Akım	Seviye	Akım	Seviye	Akım	Seviye	Akım
17	0.010	37	2.0	150	71.0	200	110.
20	0.050	46	4.3	160	78.5	240	140.
23	0.160	60	9.6	170	0.000	250	150.
26	0.390	80	20.0	180	93.0	300	199.
30	0.800	110	39.0	190	100.	350	245.

Akımlar 01 Ekim 2005 'den 30 Eylül 2006' a kadar m3/sn olarak

Gün	Ekim	Kasım	Aralık	Ocak	Şubat	Mart	Nisan	Mayıs	Haziran	Temmuz	Ağustos	Eylül
01	0.190	0.247	0.303	0.925	0.580	5.28	3.20	1.23	1.42	0.800	0.247	0.190
02	0.190	0.247	0.303	0.800	0.507	4.30	2.95	1.23	0.925	0.925	0.190	0.190
03	0.247	0.247	0.360	0.690	0.690	3.70	2.95	1.05	0.800	0.925	0.247	0.190
04	0.303	0.433	0.360	0.690	1.05	3.20	2.70	1.05	0.690	0.580	0.247	0.190
05	0.247	0.690	0.360	0.580	0.925	2.95	2.47	1.05	0.690	0.507	0.247	0.190
06	0.190	0.580	0.360	0.580	0.925	2.95	2.47	1.05	0.690	0.507	0.190	0.190
07	0.190	0.360	0.303	0.580	2.47	2.70	2.47	1.05	0.690	0.433	0.190	0.190
08	0.190	0.360	0.303	0.580	1.80	2.70	2.47	1.05	0.690	0.433	0.190	0.190
09	0.190	0.360	0.360	0.580	1.80	2.70	2.23	1.05	1.05	0.433	0.190	0.190
10	0.190	0.360	0.360	0.580	1.42	2.47	2.70	1.05	1.42	0.433	0.190	0.190
11	0.190	0.360	0.360	0.580	5.95	2.00	4.00	1.05	0.800	0.433	0.190	0.247
12	0.190	0.360	0.360	0.580	4.00	2.00	2.47	1.05	0.800	0.360	0.190	0.303
13	0.190	0.360	0.360	0.580	2.70	2.00	2.23	1.05	0.690	0.360	0.190	0.247
14	0.247	0.360	0.360	0.690	2.47	1.80	2.23	1.05	0.690	0.360	0.190	0.247
15	0.247	0.360	0.360	0.690	2.00	1.80	2.00	1.05	0.690	0.360	0.190	0.247
16	0.303	0.360	0.360	0.690	1.80	2.00	2.00	1.23	0.690	0.303	0.190	0.247
17	0.360	0.360	0.360	0.580	2.00	2.23	2.00	2.00	0.690	0.303	0.190	0.190
18	0.360	0.360	0.360	0.580	2.70	2.23	1.80	4.00	0.580	0.303	0.190	0.190
19	0.360	0.360	0.360	0.580	7.87	4.00	1.60	1.60	0.580	0.303	0.190	0.190
20	0.303	0.360	0.507	0.690	8.73	4.63	1.60	1.42	0.580	0.303	0.190	0.190
21	0.303	2.47	0.507	0.507	8.30	4.00	1.60	1.42	0.580	0.303	0.190	0.190
22	0.247	5.95	0.433	0.580	7.43	3.20	1.60	1.23	0.580	0.303	0.190	0.360
23	0.247	0.690	0.433	0.580	7.00	2.95	1.60	1.23	0.580	0.303	0.190	0.303
24	0.247	0.507	0.433	0.580	7.00	2.47	1.60	1.23	0.580	0.303	0.190	0.360
25	0.247	0.507	0.433	0.507	8.30	3.45	1.60	1.23	0.507	0.303	0.190	0.247
26	0.247	0.925	0.360	0.507	7.43	4.63	1.60	1.23	0.507	0.247	0.190	0.800
27	0.247	0.690	0.247	0.580	6.30	8.73	1.60	2.95	0.507	0.247	0.190	0.360
28	0.247	0.580	0.247	0.507	5.28	7.87	1.42	2.00	0.507	0.190	0.190	0.247
29	0.247	0.360	0.360	0.507	-----	5.95	1.42	1.60	0.925	0.190	0.190	0.247
30	0.247	0.360	0.580	0.580	-----	4.63	1.42	1.60	2.00	0.247	0.190	0.190
31	0.303	-----	0.925	0.580	-----	3.70	-----	1.60	-----	0.247	0.190	-----
Maks.	0.507	6.30	0.925	0.925	13.9	19.5	7.00	12.6	9.17	2.23	0.247	1.60
Min.	0.190	0.247	0.247	0.433	0.433	1.80	1.42	0.925	0.507	0.190	0.190	0.190
Ortalama	0.249	0.684	0.390	0.608	3.91	3.52	2.13	1.41	0.771	0.395	0.197	0.250
LT/SN/Km2	0.960	2.64	1.50	2.35	15.1	13.6	8.24	5.44	2.98	1.53	0.762	0.966
AKIM mm.	2.57	6.85	4.03	6.28	36.5	36.4	21.3	14.6	7.72	4.09	2.04	2.50
MİL. M3	0.666	1.77	1.04	1.63	9.45	9.44	5.53	3.77	2.00	1.06	0.529	0.648

SU YILI (2006) YILLIK TOPLAM AKIM 37.53 MİLYON M3 145 MM. 4.6 LT/SN/Km2

14. Yesilırmak Havzasi

D14A023 MECİTÖZÜ Ç. KALEBOĞAZI

YERİ : AMASYA-MECİTÖZÜ YOLUNUN 30. KM SOLA AYRILAN YOLUN 2.5 KM KALEBOĞAZI KÖYÜNÜN 500 M MANSABINDADIR. 25 LİK PAFTADAKİ YERİ : G35-D4
35°33'34" Doğu - 40°33'7" Kuzey

YAĞIŞ ALANI : 504,80 km2 **YAKLAŞIK KOT :** 504 m

GÖZLEM SÜRESİ : 01.10.1964 - 30.09.2006

ORTALAMA AKIMLAR : Gözlem süresinde 0.806 m3/sn. (41 Yıllık) 2006 Su yılında 0.335 m3/sn.

ANLIK EN ÇOK VE EN AZ AKIMLAR:

2006 Su yılında anlık ençok akım	:	3.30	m3/sn	28.03.2006
2006 Su yılında anlık enaz akım	:	0.007	m3/sn	01.10.2005
Gözlem süresinde anlık ençok akım	:	128.	m3/sn	11.09.2002
Gözlem süresinde anlık enaz akım	:	0.000	m3/sn	18.07.1970

20. Anahtar Eğrisi (Seviyeler cm olarak)

Seviye	Akım	Seviye	Akım	Seviye	Akım	Seviye	Akım
1	0.000	11	0.090	25	0.800	81	7.7
3	0.003	13	0.134	36	1.8	91	9.3
5	0.013	15	0.200	47	3.1	101	11.0
7	0.030	17	0.280	61	4.9	131	16.0
9	0.055	21	0.490	71	6.2	151	20.0

Akımlar 01 Ekim 2005 'den 30 Eylül 2006' a kadar m3/sn olarak

Gün	Ekim	Kasım	Aralık	Ocak	Şubat	Mart	Nisan	Mayıs	Haziran	Temmuz	Ağustos	Eylül
01	0.007	0.090	0.330	0.330	0.380	1.75	1.75	0.134	0.055	0.030	0.013	0.013
02	0.007	0.090	0.280	0.330	0.380	1.75	1.75	0.134	0.041	0.021	0.013	0.013
03	0.013	0.072	0.280	0.330	0.380	1.88	1.64	0.134	0.041	0.021	0.013	0.013
04	0.007	0.090	0.280	0.330	0.380	1.75	1.64	0.134	0.041	0.021	0.013	0.013
05	0.007	0.110	0.280	0.280	0.380	2.01	1.53	0.055	0.041	0.021	0.013	0.013
06	0.007	0.090	0.280	0.280	0.380	1.64	1.42	0.041	0.041	0.021	0.013	0.013
07	0.007	0.090	0.330	0.280	0.380	1.64	1.20	0.041	0.030	0.021	0.013	0.013
08	0.013	0.110	0.330	0.280	0.435	1.31	1.07	0.041	0.030	0.021	0.013	0.013
09	0.021	0.110	0.330	0.280	0.435	1.31	1.07	0.041	0.030	0.021	0.013	0.013
10	0.021	0.090	0.280	0.280	0.435	1.31	1.00	0.041	0.030	0.021	0.013	0.013
11	0.030	0.090	0.200	0.280	0.435	1.31	0.933	0.041	0.021	0.021	0.013	0.013
12	0.030	0.090	0.200	0.280	0.600	1.07	0.933	0.041	0.021	0.021	0.013	0.013
13	0.030	0.090	0.250	0.280	1.07	1.00	0.867	0.041	0.021	0.013	0.013	0.013
14	0.030	0.110	0.250	0.280	0.867	1.00	0.867	0.041	0.021	0.013	0.013	0.013
15	0.041	0.090	0.250	0.280	0.867	1.00	0.800	0.055	0.021	0.013	0.013	0.013
16	0.041	0.090	0.250	0.280	0.867	1.00	0.600	0.041	0.021	0.013	0.013	0.013
17	0.041	0.072	0.250	0.166	0.867	1.00	0.600	0.041	0.021	0.013	0.013	0.013
18	0.055	0.072	0.250	0.166	0.867	1.13	0.490	0.041	0.021	0.013	0.013	0.013
19	0.055	0.072	0.250	0.166	0.867	1.42	0.490	0.055	0.021	0.013	0.013	0.013
20	0.072	0.090	0.250	0.200	0.867	1.64	0.380	0.055	0.021	0.013	0.013	0.013
21	0.072	0.090	0.250	0.200	0.867	1.75	0.380	0.055	0.021	0.013	0.013	0.013
22	0.090	0.090	0.280	0.110	0.867	2.52	0.280	0.041	0.021	0.013	0.013	0.013
23	0.110	0.090	0.280	0.090	0.867	2.75	0.280	0.041	0.021	0.013	0.013	0.013
24	0.110	0.110	0.280	0.134	0.867	2.52	0.280	0.072	0.021	0.013	0.013	0.013
25	0.134	0.134	0.280	0.250	0.867	2.14	0.200	0.055	0.021	0.013	0.013	0.013
26	0.134	0.134	0.280	0.250	0.933	2.27	0.200	0.055	0.021	0.013	0.013	0.013
27	0.110	0.200	0.280	0.250	1.07	2.63	0.200	0.041	0.021	0.013	0.013	0.041
28	0.090	0.330	0.330	0.250	1.42	2.75	0.134	0.041	0.021	0.013	0.013	0.041
29	0.090	0.330	0.330	0.280	-----	2.27	0.134	0.055	0.021	0.013	0.013	0.041
30	0.110	0.330	0.330	0.380	-----	2.01	0.134	0.090	0.021	0.013	0.013	0.041
31	0.110	-----	0.330	0.380	-----	1.75	-----	0.072	-----	0.013	0.013	-----
Maks.	0.134	0.330	0.330	0.380	1.42	3.30	2.01	0.134	0.072	0.055	0.013	0.041
Min.	0.007	0.072	0.200	0.090	0.380	1.00	0.134	0.041	0.007	0.013	0.013	0.013
Ortalama	0.055	0.122	0.279	0.257	0.711	1.72	0.775	0.060	0.027	0.016	0.013	0.017
LT/SN/Km2	0.108	0.241	0.553	0.508	1.41	3.40	1.54	0.119	0.053	0.032	0.026	0.033
AKIM mm.	0.290	0.624	1.48	1.36	3.41	9.12	3.98	0.319	0.137	0.087	0.069	0.086
MİL. M3	0.146	0.315	0.747	0.687	1.72	4.60	2.01	0.161	0.069	0.044	0.035	0.043

SU YILI (2006) YILLIK TOPLAM AKIM 10.58 MİLYON M3 21 MM. 0.7 LT/SN/Km2

14. Yesilırmak Havzasi

D14A024 DELİ Ç. MAHMATLAR

YERİ : AMASYA-TURHAL YOLUNUN 22. KM SOLA AYRILAN MAHMATLAR KÖYÜNDEDİR. 25 LİK PAFTADAKİ YERİ: G35-C3
35°53'9" Doğu - 40°34'7" Kuzey

YAĞIŞ ALANI : 341,40 km2 **YAKLAŞIK KOT** : 502 m

GÖZLEM SÜRESİ : 01.10.1966 - 30.09.2006

ORTALAMA AKIMLAR : Gözlem süresinde 1.533 m3/sn. (36 Yıllık) 2006 Su yılında 0.487 m3/sn.

ANLIK EN ÇOK VE EN AZ AKIMLAR:

2006 Su yılında anlık ençok akım	:	8.89	m3/sn	26.04.2006
2006 Su yılında anlık enaz akım	:	0.000	m3/sn	16.06.2006
Gözlem süresinde anlık ençok akım	:	81.3	m3/sn	27.05.2000
Gözlem süresinde anlık enaz akım	:	0.000	m3/sn	10.07.1970

21. Anahtar Eğrisi (Seviyeler cm olarak)

Seviye	Akım	Seviye	Akım	Seviye	Akım	Seviye	Akım
1	0.000	18	1.0	91	16.4	171	50.0
4	0.024	24	1.7	101	20.0	201	66.0
7	0.110	36	3.4	111	23.5	231	83.0
10	0.270	45	5.0	121	27.0	261	100.
13	0.510	61	8.2	151	40.0	301	130.

Akımlar 01 Ekim 2005 'den 30 Eylül 2006' a kadar m3/sn olarak

Gün	Ekim	Kasım	Aralık	Ocak	Şubat	Mart	Nisan	Mayıs	Haziran	Temmuz	Ağustos	Eylül
01	0.330	0.400	0.480	0.480	0.400	1.70	1.23	0.205	0.600	0.890	KURU	KURU
02	0.330	0.400	0.480	0.480	0.400	1.70	5.80	0.205	0.420	0.780	KURU	KURU
03	0.400	0.400	0.480	0.480	0.400	1.70	5.20	0.154	0.205	0.420	KURU	KURU
04	0.400	0.400	0.480	0.480	0.400	1.70	2.10	0.110	0.074	0.350	KURU	KURU
05	0.330	0.400	0.480	0.480	0.480	1.47	1.58	0.110	0.074	0.270	KURU	KURU
06	0.330	0.400	0.480	0.480	0.590	1.23	1.47	0.110	0.046	0.205	KURU	KURU
07	0.330	0.400	0.480	0.480	0.590	1.23	1.35	0.110	0.046	0.154	KURU	KURU
08	0.330	0.400	0.480	0.480	0.590	1.10	1.10	0.154	0.046	0.110	KURU	KURU
09	0.330	0.400	0.480	0.480	0.590	1.00	1.35	0.110	0.010	0.046	KURU	KURU
10	0.330	0.400	0.480	0.480	0.590	1.00	1.47	0.110	0.010	0.046	KURU	KURU
11	0.330	0.400	0.480	0.480	0.693	0.690	2.76	0.110	0.010	0.024	KURU	KURU
12	0.330	0.400	0.480	0.480	1.03	0.510	1.83	0.110	0.010	0.010	KURU	KURU
13	0.260	0.400	0.480	0.480	0.797	0.510	1.58	0.110	0.010	0.002	KURU	KURU
14	0.202	0.400	0.480	0.480	0.797	0.600	1.58	0.154	0.010	0.002	KURU	KURU
15	0.202	0.400	0.480	0.480	0.797	0.690	1.58	0.350	0.010	0.002	KURU	KURU
16	0.260	0.400	0.480	0.480	0.590	0.600	1.47	0.420	KURU	KURU	KURU	KURU
17	0.330	0.400	0.480	0.480	0.590	0.600	1.35	1.47	KURU	KURU	KURU	KURU
18	0.330	0.400	0.480	0.480	0.590	0.510	1.23	2.10	KURU	KURU	KURU	KURU
19	0.330	0.400	0.480	0.480	0.590	0.600	1.00	1.70	KURU	KURU	KURU	KURU
20	0.330	0.400	0.480	0.480	0.797	0.600	0.890	1.23	KURU	KURU	KURU	KURU
21	0.330	0.480	0.480	0.480	0.797	0.690	0.890	0.890	KURU	KURU	KURU	0.002
22	0.330	0.590	0.480	0.480	0.693	1.35	0.890	0.890	KURU	KURU	KURU	0.154
23	0.330	0.590	0.480	0.480	0.693	1.23	0.690	0.780	KURU	KURU	KURU	0.110
24	0.330	0.480	0.480	0.480	0.693	1.23	0.690	0.600	KURU	KURU	KURU	0.110
25	0.400	0.480	0.480	0.480	0.797	1.47	0.780	0.510	KURU	KURU	KURU	0.154
26	0.400	0.480	0.480	0.480	1.70	1.58	0.690	0.510	KURU	KURU	KURU	0.690
27	0.400	0.480	0.480	0.400	1.70	1.47	0.600	0.780	KURU	KURU	KURU	0.350
28	0.400	0.480	0.480	0.400	1.70	1.58	0.510	0.890	KURU	KURU	KURU	0.350
29	0.400	0.480	0.480	0.400	-----	1.35	0.350	1.00	KURU	KURU	KURU	0.420
30	0.400	0.480	0.480	0.400	-----	1.23	0.270	0.890	KURU	KURU	KURU	0.420
31	0.400	-----	0.480	0.400	-----	1.23	-----	0.890	-----	KURU	KURU	-----
Maks.	0.480	0.590	0.480	0.480	1.70	2.76	8.89	2.10	0.600	1.10	KURU	0.690
Min.	0.202	0.400	0.480	0.400	0.400	0.420	0.270	0.110	KURU	KURU	KURU	KURU
Ortalama	0.338	0.434	0.480	0.467	0.753	1.10	1.48	0.573	0.053	0.107	KURU	0.092
LT/SN/Km2	0.989	1.27	1.41	1.37	2.20	3.23	4.32	1.68	0.154	0.313	0.000	0.269
AKIM mm.	2.65	3.30	3.77	3.66	5.33	8.64	11.2	4.50	0.400	0.838	0.000	0.698
MİL. M3	0.904	1.12	1.29	1.25	1.82	2.95	3.83	1.53	0.137	0.286	0.000	0.238

SU YILI (2006) YILLIK TOPLAM AKIM 15.35 MİLYON M3 45 MM. 1.4 LT/SN/Km2

14. Yesilırmak Havzasi

D14A033 KOŞMASAT D. ÖZBEYLİ

YERİ : **GÜMÜŞHANE KELKİT YOLUNDA KÖSE İLÇESİNİN 3.KM SİNDEN SOLA AYRILAN YOLUN 4.KM SİNDE ÖZBEYLİ KÖYÜNDE SAĞ SAHİLDEDİR.**
39°42'30" Doğu - 40°12'0" Kuzey

YAĞIŞ ALANI : **114,10 km2** **YAKLAŞIK KOT : 1558 m**

GÖZLEM SÜRESİ : **12.06.1983 - 30.09.2006**

ORTALAMA AKIMLAR : **Gözlem süresinde 0.492 m3/sn. (23 Yıllık) 2006 Su yılında 0.630 m3/sn.**

ANLIK EN ÇOK VE EN AZ AKIMLAR:

2006 Su yılında anlık ençok akım	:	**7.50**	**m3/sn**	**28.06.2006**
2006 Su yılında anlık enaz akım	:	**0.082**	**m3/sn**	**26.06.2006**
Gözlem süresinde anlık ençok akım	:	**19.5**	**m3/sn**	**11.06.1973**
Gözlem süresinde anlık enaz akım	:	**0.000**	**m3/sn**	**14.08.1971**

Akımlar 01 Ekim 2005 'den 30 Eylül 2006' a kadar m3/sn olarak

Gün	Ekim	Kasım	Aralık	Ocak	Şubat	Mart	Nisan	Mayıs	Haziran	Temmuz	Ağustos	Eylül
01	0.320	1.50	0.260	0.225	0.180	0.260	1.71	3.45	0.570	0.500	0.180	0.140
02	0.260	1.29	0.260	0.225	0.180	0.320	1.93	4.10	0.570	0.500	0.180	0.140
03	0.180	1.29	0.260	0.180	0.180	0.375	2.54	3.84	0.570	0.500	0.140	0.140
04	0.180	1.18	0.260	0.180	0.180	0.430	2.41	3.58	0.570	0.500	0.140	0.140
05	0.180	0.640	0.260	0.180	0.180	0.430	2.28	3.32	0.430	0.500	0.140	0.180
06	0.180	0.570	0.225	0.180	0.180	0.430	2.04	2.93	0.430	0.500	0.106	0.180
07	0.180	0.570	0.225	0.180	0.180	0.904	1.93	2.67	0.375	0.500	0.106	0.180
08	0.180	0.500	0.225	0.180	0.180	1.71	2.04	3.58	0.375	0.430	0.140	0.180
09	0.180	0.500	0.225	0.180	0.180	1.82	2.15	3.97	0.375	0.375	0.140	0.180
10	0.180	0.430	0.225	0.180	0.180	1.29	2.28	3.71	0.320	0.375	0.140	0.180
11	0.180	0.430	0.225	0.180	0.140	1.18	2.54	2.93	0.260	0.430	0.140	0.180
12	0.180	0.375	0.225	0.225	0.140	1.18	2.54	2.28	0.260	0.430	0.140	0.180
13	0.180	0.320	0.225	0.225	0.140	1.08	2.28	2.15	0.180	0.375	0.140	0.180
14	0.225	0.320	0.225	0.225	0.140	1.08	2.15	1.93	0.106	0.320	0.106	0.180
15	0.225	0.320	0.225	0.180	0.140	1.08	1.60	1.71	0.180	0.320	0.106	0.140
16	0.225	0.260	0.225	0.180	0.140	1.08	1.39	1.60	0.180	0.320	0.140	0.140
17	0.225	0.260	0.225	0.180	0.140	1.08	1.29	1.50	0.180	0.140	0.140	0.140
18	0.225	0.260	0.225	0.180	0.140	1.08	1.18	1.39	0.180	0.180	0.140	0.140
19	0.260	0.260	0.225	0.180	0.140	1.08	1.08	1.29	0.180	0.140	0.375	0.140
20	0.320	0.260	0.225	0.180	0.140	1.18	0.992	1.18	0.180	0.140	0.375	0.140
21	0.260	0.260	0.225	0.180	0.140	1.18	1.08	0.992	0.140	0.140	0.260	0.140
22	0.225	0.260	0.225	0.180	0.140	1.18	1.93	0.904	0.140	0.140	0.180	0.140
23	0.225	0.260	0.225	0.180	0.140	1.18	2.41	0.904	0.106	0.140	0.140	0.180
24	0.225	0.260	0.225	0.180	0.140	1.18	3.06	0.816	0.106	0.140	0.140	0.180
25	0.225	0.260	0.225	0.180	0.180	1.29	2.41	0.816	0.106	0.140	0.106	0.180
26	0.225	0.260	0.225	0.180	0.180	1.60	1.93	0.816	0.320	0.225	0.140	0.180
27	0.225	0.260	0.225	0.180	0.225	2.04	1.82	0.904	0.320	0.180	0.140	0.180
28	0.225	0.260	0.225	0.180	0.225	1.82	1.50	0.904	2.67	0.180	0.140	0.225
29	0.320	0.260	0.225	0.180	-----	1.71	1.60	0.728	1.18	0.180	0.140	0.225
30	1.50	0.260	0.225	0.180	-----	1.71	3.32	0.640	0.500	0.180	0.140	0.225
31	1.82	-----	0.225	0.180	-----	1.71	-----	0.570	-----	0.180	0.140	-----
Maks.	2.04	1.50	0.260	0.225	0.225	2.28	3.84	4.36	7.50	0.500	0.430	0.225
Min.	0.140	0.260	0.225	0.180	0.140	0.225	0.992	0.570	0.082	0.140	0.106	0.140
Ortalama	0.314	0.471	0.231	0.187	0.163	1.15	1.98	2.00	0.402	0.300	0.157	0.168
LT/SN/Km2	2.75	4.13	2.02	1.64	1.43	10.1	17.4	17.6	3.52	2.63	1.38	1.48
AKIM mm.	7.38	10.7	5.41	4.40	3.46	27.0	45.0	47.0	9.13	7.04	3.70	3.83
MİL. M3	0.842	1.22	0.618	0.502	0.395	3.08	5.13	5.37	1.04	0.804	0.422	0.437

SU YILI (2006) YILLIK TOPLAM AKIM 19.86 MİLYON M3 174 MM. 5.5 LT/SN/Km2

14. Yesilırmak Havzasi

D14A050 DÖVENCİ DERESİ FİDANLIK

YERİ : **ÇORUM-ALACA YOLUNUN 24. KM SİNDEKİ BÜYÜK ELBİZ KÖYÜNE 500 M. MESAFEDEKİ TAŞKÖPRÜNÜN 4 KM. MANSABINDADIR.**
35°14'42" Doğu - 40°42'14" Kuzey

YAĞIŞ ALANI : **150.40 km2** **YAKLAŞIK KOT : 1005 m**

GÖZLEM SÜRESİ : **13.07.1966 - 30.09.2006**

ORTALAMA AKIMLAR : **Gözlem süresinde 0.428 m3/sn. (28 Yıllık) 2006 Su yılında 0.357 m3/sn.**

ANLIK EN ÇOK VE EN AZ AKIMLAR:

2006 Su yılında anlık ençok akım	:	**6.26**	**m3/sn**	**04.03.2006**
2006 Su yılında anlık enaz akım	:	**0.000**	**m3/sn**	**31.10.2005**
Gözlem süresinde anlık ençok akım	:	**31.0**	**m3/sn**	**16.06.1967**
Gözlem süresinde anlık enaz akım	:	**0.000**	**m3/sn**	**24.08.1976**

İstasyon için kullanılmış anahtar bulunamadı.

Akımlar 01 Ekim 2005 'den 30 Eylül 2006' a kadar m3/sn olarak

Gün	Ekim	Kasım	Aralık	Ocak	Şubat	Mart	Nisan	Mayıs	Haziran	Temmuz	Ağustos	Eylül
01	KURU	KURU	KURU	KURU	0.022	2.98	1.58	0.664	0.212	0.071	KURU	KURU
02	KURU	KURU	KURU	KURU	0.022	4.46	1.36	0.596	0.175	0.071	KURU	KURU
03	KURU	KURU	KURU	KURU	0.022	5.36	1.16	0.596	0.175	0.054	KURU	KURU
04	KURU	KURU	KURU	KURU	0.022	6.26	1.07	0.800	0.175	0.054	KURU	KURU
05	KURU	KURU	KURU	KURU	0.022	3.30	1.25	0.732	0.142	0.041	KURU	KURU
06	KURU	KURU	KURU	KURU	0.022	2.98	1.16	0.732	0.142	0.030	KURU	KURU
07	KURU	KURU	KURU	KURU	0.022	2.66	1.07	0.596	0.115	0.030	KURU	KURU
08	KURU	KURU	KURU	0.010	0.022	2.82	1.07	0.664	0.115	0.030	KURU	KURU
09	KURU	KURU	KURU	0.010	0.022	2.98	0.980	0.528	0.091	0.030	KURU	KURU
10	KURU	KURU	KURU	0.010	0.022	2.08	0.980	0.460	0.091	0.022	KURU	KURU
11	KURU	KURU	KURU	0.015	0.022	1.80	0.980	0.460	0.091	0.022	KURU	KURU
12	KURU	KURU	KURU	0.022	0.022	1.47	0.980	0.350	0.091	0.022	KURU	KURU
13	KURU	KURU	KURU	0.022	0.041	1.47	0.890	0.350	0.091	0.022	KURU	KURU
14	KURU	KURU	KURU	0.022	0.041	1.47	0.890	0.310	0.091	0.015	KURU	KURU
15	KURU	KURU	KURU	0.022	0.071	1.69	0.890	0.310	0.091	0.010	KURU	KURU
16	KURU	KURU	KURU	0.022	0.071	1.58	0.890	0.212	0.091	0.006	KURU	KURU
17	KURU	KURU	KURU	0.022	0.071	1.47	0.890	0.212	0.091	0.003	KURU	KURU
18	KURU	KURU	KURU	0.022	0.071	1.58	0.800	0.255	0.071	0.003	KURU	KURU
19	KURU	KURU	KURU	0.022	0.071	1.94	0.732	0.255	0.071	0.003	KURU	KURU
20	KURU	KURU	KURU	0.030	0.115	2.08	0.732	0.212	0.054	0.003	KURU	KURU
21	KURU	KURU	KURU	0.030	0.142	2.08	0.732	0.175	0.054	0.003	KURU	KURU
22	KURU	KURU	KURU	0.030	0.310	2.08	0.732	0.175	0.054	0.003	KURU	KURU
23	KURU	KURU	KURU	0.030	0.528	2.36	0.664	0.175	0.041	0.003	KURU	KURU
24	KURU	KURU	KURU	0.030	0.800	2.50	0.664	0.175	0.041	0.006	KURU	KURU
25	KURU	KURU	KURU	0.030	1.58	2.82	0.664	0.175	0.041	0.006	KURU	KURU
26	KURU	KURU	KURU	0.022	2.22	2.66	0.664	0.175	0.041	0.003	KURU	KURU
27	KURU	KURU	KURU	0.022	2.22	2.66	0.596	0.212	0.041	KURU	KURU	KURU
28	KURU	KURU	KURU	0.022	1.94	2.22	0.596	0.255	0.041	KURU	KURU	KURU
29	KURU	KURU	KURU	0.022	-----	1.94	0.596	0.255	0.115	KURU	KURU	KURU
30	KURU	KURU	KURU	0.022	-----	1.80	0.596	0.212	0.142	KURU	KURU	KURU
31	KURU	-----	KURU	0.022	-----	1.80	-----	0.212	-----	KURU	KURU	-----
Maks.	KURU	KURU	KURU	0.030	2.22	6.26	1.58	0.800	0.212	0.071	KURU	KURU
Min.	KURU	KURU	KURU	KURU	0.022	1.47	0.596	0.175	0.041	KURU	KURU	KURU
Ortalama	KURU	KURU	KURU	0.017	0.377	2.50	0.895	0.371	0.096	0.018	KURU	KURU
LT/SN/Km2	0.000	0.000	0.000	0.114	2.51	16.6	5.95	2.46	0.638	0.121	0.000	0.000
AKIM mm.	0.000	0.000	0.000	0.306	6.06	44.4	15.4	6.60	1.65	0.325	0.000	0.000
MİL. M3	0.000	0.000	0.000	0.046	0.912	6.68	2.32	0.993	0.249	0.049	0.000	0.000

SU YILI (2006) YILLIK TOPLAM AKIM 11.25 MİLYON M3 75 MM. 2.4 LT/SN/Km2

14. Yesilırmak Havzasi

D14A062 SARSI D. ARTOVA

YERİ : ARTOVA-SARSI YOLUNUN 1 KM MENFEZDEDİR. 25 LIK PAFTADAKİ YERİ: H36-C4
36°16'26" Doğu - 40°6'56" Kuzey

YAĞIŞ ALANI : 21,50 km2 **YAKLAŞIK KOT :** 1232 m

GÖZLEM SÜRESİ : 01.10.1967 - 30.09.2006

ORTALAMA AKIMLAR : Gözlem süresinde 0.118 m3/sn. (19 Yıllık) 2006 Su yılında 0.034 m3/sn.

ANLIK EN ÇOK VE EN AZ AKIMLAR:

2006 Su yılında anlık ençok akım	:	0.560	m3/sn	14.07.2006
2006 Su yılında anlık enaz akım	:	0.000	m3/sn	31.07.2006
Gözlem süresinde anlık ençok akım	:	20.0	m3/sn	19.05.1971
Gözlem süresinde anlık enaz akım	:	0.000	m3/sn	22.08.1998

17. Anahtar Eğrisi (Seviyeler cm olarak)

Seviye	Akım	Seviye	Akım	Seviye	Akım	Seviye	Akım
1	0.000	11	0.184	35	2.0	140	19.5
3	0.001	13	0.290	42	2.8	170	26.0
5	0.014	18	0.560	60	5.2	180	28.0
7	0.046	23	0.910	80	8.4	190	30.0
9	0.100	29	1.5	100	12.0	200	32.0

Akımlar 01 Ekim 2005 'den 30 Eylül 2006' a kadar m3/sn olarak

Gün	Ekim	Kasım	Aralık	Ocak	Şubat	Mart	Nisan	Mayıs	Haziran	Temmuz	Ağustos	Eylül
01	0.014	0.026	0.026	0.046	0.026	0.046	0.108	0.080	0.048	0.006	KURU	KURU
02	0.014	0.026	0.026	0.046	0.026	0.046	0.240	0.080	0.048	0.006	KURU	KURU
03	0.014	0.026	0.026	0.046	0.026	0.046	0.165	0.080	0.025	0.014	KURU	KURU
04	0.014	0.026	0.026	0.026	0.026	0.046	0.137	0.080	0.025	0.014	KURU	KURU
05	0.014	0.026	0.026	0.026	0.026	0.046	0.137	0.080	0.025	0.006	KURU	KURU
06	0.014	0.026	0.026	0.026	0.026	0.046	0.137	0.080	0.025	0.006	KURU	KURU
07	0.014	0.026	0.026	0.026	0.026	0.046	0.137	0.080	0.025	0.006	KURU	KURU
08	0.014	0.026	0.026	0.026	0.026	0.046	0.137	0.108	0.025	0.006	KURU	KURU
09	0.014	0.026	0.026	0.026	0.026	0.046	0.137	0.108	0.025	0.006	KURU	KURU
10	0.014	0.026	0.026	0.026	0.026	0.046	0.137	0.108	0.108	0.006	KURU	KURU
11	0.014	0.026	0.026	0.026	0.046	0.046	0.137	0.108	0.048	0.006	KURU	KURU
12	0.014	0.026	0.026	0.026	0.070	0.046	0.137	0.108	0.048	0.006	KURU	KURU
13	0.014	0.026	0.026	0.026	0.046	0.046	0.108	0.108	0.048	0.006	KURU	KURU
14	0.014	0.026	0.014	0.026	0.026	0.046	0.108	0.108	0.048	0.046	KURU	KURU
15	0.014	0.026	0.014	0.026	0.026	0.046	0.108	0.108	0.048	0.184	KURU	KURU
16	0.026	0.026	0.026	0.026	0.026	0.046	0.108	0.048	0.025	0.026	KURU	KURU
17	0.026	0.026	0.026	0.026	0.026	0.046	0.108	0.048	0.025	0.014	KURU	KURU
18	0.026	0.026	0.026	0.026	0.026	0.046	0.080	0.048	0.025	0.014	KURU	KURU
19	0.026	0.026	0.026	0.026	0.026	0.046	0.080	0.048	0.014	0.014	KURU	KURU
20	0.026	0.026	0.026	0.026	0.026	0.070	0.080	0.048	0.006	0.014	KURU	KURU
21	0.026	0.026	0.026	0.026	0.026	0.070	0.080	0.048	0.006	0.014	KURU	KURU
22	0.026	0.026	0.026	0.026	0.026	0.070	0.080	0.048	0.006	0.014	KURU	KURU
23	0.026	0.026	0.026	0.026	0.026	0.046	0.080	0.048	0.006	0.006	KURU	KURU
24	0.026	0.026	0.026	0.026	0.046	0.046	0.080	0.048	0.006	0.006	KURU	KURU
25	0.026	0.026	0.026	0.026	0.046	0.046	0.080	0.025	0.006	0.006	KURU	KURU
26	0.026	0.026	0.026	0.026	0.046	0.070	0.080	0.025	0.006	0.006	KURU	KURU
27	0.026	0.026	0.026	0.026	0.046	0.070	0.080	0.048	0.006	0.006	KURU	KURU
28	0.026	0.026	0.026	0.026	0.046	0.046	0.080	0.048	0.006	0.006	KURU	KURU
29	0.026	0.026	0.026	0.026	-----	0.046	0.080	0.048	0.006	0.006	KURU	KURU
30	0.026	0.026	0.026	0.026	-----	0.070	0.080	0.048	0.006	KURU	KURU	KURU
31	0.026	-----	0.026	0.026	-----	0.070	-----	0.048	-----	KURU	KURU	-----
Maks.	0.026	0.026	0.046	0.046	0.070	0.070	0.532	0.108	0.240	0.560	KURU	KURU
Min.	0.014	0.026	0.014	0.014	0.026	0.046	0.080	0.025	0.006	KURU	KURU	KURU
Ortalama	0.020	0.026	0.025	0.028	0.033	0.051	0.111	0.069	0.026	0.015	KURU	KURU
LT/SN/Km2	0.939	1.21	1.17	1.30	1.51	2.39	5.16	3.22	1.20	0.714	0.000	0.000
AKIM mm.	2.52	3.13	3.14	3.48	3.66	6.41	13.4	8.62	3.11	1.91	0.000	0.000
MİL. M3	0.054	0.067	0.068	0.075	0.079	0.138	0.287	0.185	0.067	0.041	0.000	0.000

SU YILI (2006) YILLIK TOPLAM AKIM 1.06 MİLYON M3 49 MM. 1.6 LT/SN/Km2

14. Yesilırmak Havzasi

D14A064 AKSU D. GÖKÇE

YERİ : **TOKAT-SİVAS KARAYOLUNUN 3 KM SAĞA AYRILAN KÖY YOLUNUN 2 KM SİNDEKİ GÖKÇE KÖYÜNDEDİR**
25 LİK PAFTADAKİ YERİ: H37-A4
36°32'24" Doğu - 40°15'5" Kuzey

YAĞIŞ ALANI : **100,00 km2** **YAKLAŞIK KOT : 825 m**

GÖZLEM SÜRESİ : **21.08.2000 - 30.09.2006**

ORTALAMA AKIMLAR : **Gözlem süresinde 0.393 m3/sn. (6 Yıllık) 2006 Su yılında 0.302 m3/sn.**

ANLIK EN ÇOK VE EN AZ AKIMLAR:

2006 Su yılında anlık ençok akım	**:**	**13.7**	**m3/sn**	**26.09.2006**
2006 Su yılında anlık enaz akım	**:**	**0.014**	**m3/sn**	**31.08.2006**
Gözlem süresinde anlık ençok akım	**:**	**13.7**	**m3/sn**	**26.09.2006**
Gözlem süresinde anlık enaz akım	**:**	**0.005**	**m3/sn**	**01.09.2004**

1. Anahtar Eğrisi (Seviyeler cm olarak)

Seviye	Akım	Seviye	Akım	Seviye	Akım	Seviye	Akım
1	0.000	11	0.130	28	1.1	74	5.4
3	0.003	14	0.240	32	1.4	90	7.0
5	0.014	16	0.340	40	2.1	110	9.1
7	0.037	20	0.550	50	3.0	130	11.4
9	0.076	25	0.880	60	4.0	150	13.7

Akımlar 01 Ekim 2005 'den 30 Eylül 2006' a kadar m3/sn olarak

Gün	Ekim	Kasım	Aralık	Ocak	Şubat	Mart	Nisan	Mayıs	Haziran	Temmuz	Ağustos	Eylül
01	0.165	0.200	0.290	0.340	0.200	0.440	0.495	0.495	0.290	0.130	0.076	0.014
02	0.165	0.200	0.290	0.290	0.340	0.440	0.495	0.495	0.240	0.130	0.037	0.024
03	0.165	0.165	0.290	0.290	0.240	0.440	0.495	0.495	0.200	0.130	0.055	0.024
04	0.165	0.165	0.290	0.290	0.200	0.440	0.495	0.495	0.165	0.100	0.055	0.024
05	0.165	0.165	0.290	0.290	0.165	0.440	0.495	0.495	0.076	0.100	0.055	0.014
06	0.165	0.165	0.290	0.290	0.165	0.440	0.495	0.495	0.055	0.100	0.055	0.024
07	0.165	0.165	0.240	0.340	0.340	0.390	0.495	0.495	0.055	0.165	0.037	0.037
08	0.165	0.165	0.240	0.340	0.290	0.390	0.495	0.550	0.055	0.076	0.037	0.037
09	0.200	0.165	0.240	0.340	0.390	0.390	0.495	0.550	0.055	0.076	0.037	0.037
10	0.200	0.165	0.240	0.340	0.340	0.390	0.495	0.495	0.290	0.055	0.037	0.037
11	0.200	0.165	0.240	0.340	0.495	0.390	0.495	0.440	0.390	0.037	0.037	0.055
12	0.200	0.165	0.240	0.290	0.670	0.390	0.495	0.440	0.340	0.024	0.037	0.100
13	0.200	0.165	0.240	0.290	0.550	0.390	0.495	0.440	0.290	0.024	0.037	0.100
14	0.200	0.165	0.240	0.290	0.495	0.390	0.495	0.440	0.290	0.024	0.055	0.100
15	0.200	0.165	0.240	0.290	0.440	0.390	0.495	0.440	0.290	0.024	0.037	0.100
16	0.240	0.165	0.340	0.290	0.440	0.390	0.495	0.440	0.290	0.024	0.024	0.130
17	0.240	0.165	0.290	0.290	0.440	0.390	0.495	0.495	0.200	0.024	0.037	0.165
18	0.240	0.165	0.290	0.290	0.340	0.390	0.495	0.495	0.165	0.024	0.055	0.165
19	0.240	0.165	0.290	0.240	0.390	0.390	0.495	0.495	0.100	0.024	0.055	0.200
20	0.240	0.165	0.290	0.240	0.390	0.390	0.440	0.495	0.076	0.024	0.055	0.165
21	0.240	0.240	0.290	0.240	0.390	0.390	0.440	0.440	0.100	0.024	0.037	0.165
22	0.240	0.240	0.290	0.200	0.390	0.390	0.440	0.440	0.100	0.024	0.024	0.200
23	0.240	0.240	0.290	0.200	0.390	0.495	0.440	0.390	0.100	0.024	0.024	0.240
24	0.240	0.240	0.290	0.200	0.390	0.440	0.440	0.390	0.100	0.037	0.037	0.340
25	0.240	0.240	0.290	0.200	0.390	0.440	0.440	0.390	0.100	0.037	0.024	0.550
26	0.240	0.240	0.290	0.200	0.390	0.495	0.440	0.390	0.076	0.055	0.037	8.10
27	0.240	0.240	0.240	0.200	0.390	0.495	0.495	0.390	0.076	0.076	0.037	6.00
28	0.240	0.240	0.240	0.200	0.390	0.495	0.495	0.390	0.076	0.076	0.024	3.95
29	0.240	0.240	0.290	0.200	-----	0.495	0.495	0.340	0.100	0.076	0.024	0.100
30	0.240	0.240	0.340	0.200	-----	0.495	0.495	0.290	0.100	0.100	0.024	0.014
31	0.240	-----	0.340	0.200	-----	0.495	-----	0.290	-----	0.076	0.014	-----
Maks.	0.240	0.240	0.610	0.390	0.670	0.495	0.495	0.610	0.610	0.165	0.100	13.7
Min.	0.165	0.165	0.240	0.200	0.165	0.390	0.440	0.290	0.055	0.024	0.014	0.014
Ortalama	0.212	0.192	0.277	0.266	0.373	0.427	0.482	0.446	0.161	0.062	0.039	0.707
LT/SN/Km2	2.12	1.92	2.77	2.66	3.73	4.27	4.82	4.46	1.61	0.619	0.392	7.07
AKIM mm.	5.67	4.99	7.42	7.12	9.02	11.4	12.5	11.9	4.18	1.66	1.05	18.3
MİL. M3	0.567	0.499	0.742	0.712	0.902	1.14	1.25	1.19	0.418	0.166	0.105	1.83

SU YILI (2006) YILLIK TOPLAM AKIM 9.52 MİLYON M3 95 MM. 3.0 LT/SN/Km2

14. Yesilırmak Havzasi

D14A080 GÜNDELEN D. KIZILLI

YERİ : **AKDAĞMADENİ SİVAS YOLUNUN 26.KM SİNDEKİ KÖPRÜNÜN 1 KM MENBASINDADIR**
36°2'18" Doğu - 39°47'57" Kuzey

YAĞIŞ ALANI : **338,60 km2** **YAKLAŞIK KOT : 1193 m**

GÖZLEM SÜRESİ : **13.08.1969 - 30.09.2006**

ORTALAMA AKIMLAR : **Gözlem süresinde 1.381 m3/sn. (37 Yıllık) 2006 Su yılında 0.623 m3/sn.**

ANLIK EN ÇOK VE EN AZ AKIMLAR:

2006 Su yılında anlık ençok akım	**:**	**1.88**	**m3/sn**	**17.05.2006**
2006 Su yılında anlık enaz akım	**:**	**0.004**	**m3/sn**	**12.09.2006**
Gözlem süresinde anlık ençok akım	**:**	**26.0**	**m3/sn**	**04.05.1980**
Gözlem süresinde anlık enaz akım	**:**	**0.000**	**m3/sn**	**21.08.1994**

9. Anahtar Eğrisi (Seviyeler cm olarak)

Seviye	Akım	Seviye	Akım	Seviye	Akım	Seviye	Akım
14	0.004	24	0.225	45	1.7	90	13.0
16	0.018	26	0.330	50	2.5	100	17.0
18	0.050	28	0.390	60	4.1	110	21.0
20	0.089	30	0.492	70	6.3	120	25.0
22	0.150	40	1.2	80	9.2	121	25.4

Akımlar 01 Ekim 2005 'den 30 Eylül 2006' a kadar m3/sn olarak

Gün	Ekim	Kasım	Aralık	Ocak	Şubat	Mart	Nisan	Mayıs	Haziran	Temmuz	Ağustos	Eylül
01	0.577	0.390	0.492	0.356	0.390	0.841	1.40	1.40	1.19	0.492	0.150	0.018
02	0.577	0.390	0.423	0.356	0.390	0.911	1.40	1.51	1.12	0.423	0.150	0.018
03	0.577	0.390	0.423	0.390	0.390	0.911	1.30	1.51	1.12	0.390	0.150	0.018
04	0.628	0.390	0.423	0.390	0.390	0.911	1.40	1.51	1.12	0.356	0.150	0.013
05	0.577	1.05	0.423	0.390	0.423	0.911	1.51	1.40	1.05	0.330	0.089	0.013
06	0.390	0.841	0.423	0.423	0.390	0.981	1.51	1.40	0.981	0.330	0.070	0.013
07	0.390	0.701	0.423	0.632	0.423	0.911	1.40	1.51	0.981	0.269	0.050	0.013
08	0.390	0.701	0.423	0.632	0.423	0.841	1.30	1.61	0.911	0.225	0.018	0.013
09	0.390	0.701	0.423	0.562	0.423	0.771	1.30	1.51	0.911	0.225	0.018	0.013
10	0.390	0.701	0.423	0.492	0.492	0.771	1.30	1.51	0.911	0.180	0.018	0.013
11	0.390	0.562	0.390	0.492	0.492	0.841	1.40	1.51	0.911	0.150	0.018	0.013
12	0.390	0.492	0.390	0.492	0.562	0.911	1.40	1.61	0.841	0.150	0.030	0.004
13	0.356	0.492	0.390	0.492	0.562	0.911	1.30	1.72	0.841	0.180	0.030	0.013
14	0.356	0.492	0.390	0.423	0.562	0.981	1.30	1.72	0.841	0.180	0.030	0.013
15	0.356	0.492	0.390	0.390	0.632	0.981	1.30	1.61	0.771	0.180	0.030	0.013
16	0.390	0.492	0.423	0.390	0.701	1.05	1.40	1.72	0.701	0.180	0.030	0.013
17	0.423	0.423	0.492	0.390	0.701	1.05	1.51	1.88	0.701	0.180	0.018	0.013
18	0.423	0.390	0.492	0.390	0.771	0.981	1.51	1.72	0.632	0.180	0.018	0.013
19	0.423	0.390	0.423	0.356	0.701	0.911	1.40	1.61	0.632	0.150	0.018	0.013
20	0.423	0.423	0.423	0.390	0.701	0.911	1.51	1.61	0.632	0.150	0.018	0.013
21	0.423	0.492	0.423	0.356	0.771	1.05	1.51	1.51	0.632	0.150	0.018	0.070
22	0.423	0.632	0.390	0.356	0.771	1.05	1.51	1.51	0.632	0.150	0.030	0.225
23	0.423	0.423	0.390	0.492	0.771	1.05	1.51	1.51	0.632	0.150	0.030	0.269
24	0.423	0.390	0.390	0.492	0.841	1.05	1.51	1.40	0.632	0.150	0.030	0.269
25	0.423	0.492	0.390	0.492	0.841	1.12	1.40	1.40	0.632	0.150	0.030	0.269
26	0.423	0.492	0.390	0.492	0.771	1.12	1.40	1.30	0.562	0.150	0.030	0.269
27	0.423	0.492	0.390	0.423	0.841	1.12	1.40	1.61	0.562	0.150	0.018	0.269
28	0.390	0.492	0.390	0.390	0.771	1.19	1.30	1.61	0.562	0.150	0.018	0.269
29	0.390	0.492	0.390	0.390	-----	1.30	1.40	1.40	0.562	0.150	0.018	0.269
30	0.390	0.492	0.356	0.390	-----	1.30	1.51	1.40	0.562	0.150	0.018	0.269
31	0.390	-----	0.356	0.390	-----	1.40	-----	1.19	-----	0.150	0.018	-----
Maks.	1.40	1.19	0.562	KURU	0.841	1.40	1.51	1.88	1.19	0.492	0.150	0.269
Min.	0.356	0.390	0.356	KURU	0.390	0.771	1.30	1.19	0.562	0.150	0.013	0.004
Ortalama	0.430	0.526	0.412	0.435	0.603	1.00	1.41	1.53	0.792	0.211	0.044	0.090
LT/SN/Km2	1.27	1.55	1.22	1.29	1.78	2.96	4.16	4.52	2.34	0.624	0.130	0.267
AKIM mm.	3.40	4.03	3.26	3.44	4.31	7.92	10.8	12.1	6.06	1.67	0.347	0.692
MİL. M3	1.15	1.36	1.10	1.17	1.46	2.68	3.65	4.10	2.05	0.566	0.118	0.234

SU YILI (2006) YILLIK TOPLAM AKIM 19.64 MİLYON M3 58 MM. 1.8 LT/SN/Km2

14. Yesilırmak Havzasi

D14A081 DEREÇAM D. GÜVEN BARAJI GİRİŞİ

YERİ İLERİSİNDEDİR : **SAMSUN-HAVZA YOLUNUN 55. KM SİNDEN SAĞA AYRILAN ÇUKURSAĞI KÖYÜ YOLUNUN 1750. M**

25 LİK PAFTADAKİ YERİ: F35-C3
35°58'1" Doğu - 41°4'33" Kuzey

YAĞIŞ ALANI : **9,90 km2** **YAKLAŞIK KOT : 652 m**

GÖZLEM SÜRESİ : **01.10.1969 - 30.09.2006**

ORTALAMA AKIMLAR : **Gözlem süresinde 0.076 m3/sn. (32 Yıllık) 2006 Su yılında 0.065 m3/sn.**

ANLIK EN ÇOK VE EN AZ AKIMLAR:

2006 Su yılında anlık ençok akım	**:**	**1.38**	**m3/sn**	**27.05.2006**
2006 Su yılında anlık enaz akım	**:**	**0.001**	**m3/sn**	**09.07.2006**
Gözlem süresinde anlık ençok akım	**:**	**24.0**	**m3/sn**	**26.05.1974**
Gözlem süresinde anlık enaz akım	**:**	**0.000**	**m3/sn**	**06.10.1972**

9. Anahtar Eğrisi (Seviyeler cm olarak)

Seviye	Akım	Seviye	Akım	Seviye	Akım	Seviye	Akım
1	0.000	17	0.480	57	4.0	131	14.0
4	0.005	20	0.690	81	6.9	141	16.0
7	0.044	23	0.930	91	8.2	161	19.5
10	0.132	28	1.3	101	9.6	171	23.0
14	0.310	36	2.0	111	11.0		

Akımlar 01 Ekim 2005 'den 30 Eylül 2006' a kadar m3/sn olarak

Gün	Ekim	Kasım	Aralık	Ocak	Şubat	Mart	Nisan	Mayıs	Haziran	Temmuz	Ağustos	Eylül
01	0.012	0.012	0.025	0.025	0.012	0.260	0.215	0.070	0.132	0.012	0.001	0.012
02	0.012	0.012	0.025	0.025	0.012	0.215	0.215	0.070	0.132	0.012	0.001	0.012
03	0.012	0.012	0.025	0.025	0.012	0.215	0.215	0.070	0.132	0.012	0.005	0.012
04	0.012	0.044	0.025	0.025	0.025	0.215	0.215	0.070	0.044	0.012	0.005	0.012
05	0.012	0.044	0.025	0.025	0.025	0.170	0.215	0.070	0.025	0.005	0.001	0.012
06	0.012	0.012	0.025	0.025	0.025	0.132	0.132	0.070	0.025	0.005	0.001	0.012
07	0.012	0.012	0.025	0.025	0.044	0.132	0.132	0.070	0.012	0.005	0.001	0.012
08	0.012	0.012	0.025	0.025	0.044	0.132	0.132	0.070	0.025	0.005	0.001	0.012
09	0.012	0.012	0.025	0.025	0.044	0.132	0.132	0.070	0.012	0.001	0.001	0.012
10	0.012	0.012	0.025	0.025	0.044	0.132	0.170	0.070	0.025	0.001	0.001	0.012
11	0.012	0.012	0.025	0.025	0.260	0.132	0.215	0.070	0.025	0.001	0.001	0.012
12	0.012	0.012	0.025	0.025	0.215	0.132	0.170	0.070	0.025	0.001	0.001	0.012
13	0.012	0.012	0.025	0.025	0.132	0.132	0.132	0.070	0.012	0.001	0.001	0.012
14	0.012	0.012	0.012	0.025	0.132	0.132	0.132	0.070	0.025	0.001	0.001	0.012
15	0.012	0.012	0.012	0.025	0.132	0.132	0.132	0.070	0.044	0.001	0.001	0.012
16	0.012	0.012	0.012	0.025	0.132	0.132	0.132	0.070	0.025	0.001	0.001	0.012
17	0.012	0.012	0.012	0.025	0.132	0.132	0.132	0.260	0.012	0.001	0.005	0.012
18	0.012	0.012	0.012	0.025	0.170	0.132	0.070	0.310	0.012	0.001	0.005	0.012
19	0.012	0.044	0.012	0.025	0.420	0.132	0.070	0.170	0.012	0.001	0.005	0.012
20	0.012	0.098	0.025	0.025	0.760	0.310	0.070	0.098	0.012	0.001	0.005	0.012
21	0.012	0.360	0.025	0.025	0.420	0.360	0.070	0.098	0.012	0.001	0.005	0.012
22	0.012	0.132	0.025	0.025	0.420	0.260	0.070	0.098	0.012	0.001	0.005	0.012
23	0.012	0.098	0.025	0.025	0.420	0.215	0.070	0.098	0.012	0.001	0.012	0.012
24	0.012	0.044	0.025	0.025	0.420	0.215	0.070	0.098	0.005	0.001	0.012	0.012
25	0.012	0.012	0.025	0.025	0.420	0.215	0.070	0.098	0.005	0.001	0.012	0.012
26	0.012	0.012	0.025	0.012	0.360	0.215	0.070	0.098	0.005	0.001	0.012	0.012
27	0.012	0.012	0.025	0.005	0.310	0.260	0.070	0.360	0.005	0.001	0.012	0.012
28	0.012	0.012	0.025	0.012	0.260	0.480	0.070	0.215	0.005	0.001	0.012	0.012
29	0.012	0.012	0.044	0.012	-----	0.360	0.070	0.170	0.005	0.001	0.012	0.012
30	0.012	0.012	0.044	0.012	-----	0.260	0.070	0.132	0.005	0.001	0.012	0.012
31	0.012	-----	0.044	0.012	-----	0.215	-----	0.132	-----	0.001	0.012	-----
Maks.	0.012	0.360	0.044	0.044	0.760	0.760	0.360	1.38	0.132	0.012	0.012	0.012
Min.	0.012	0.012	0.005	0.005	0.012	0.132	0.070	0.070	0.005	0.001	0.001	0.012
Ortalama	0.012	0.038	0.024	0.022	0.207	0.203	0.124	0.115	0.028	0.003	0.005	0.012
LT/SN/Km2	1.21	3.80	2.46	2.25	20.9	20.5	12.6	11.6	2.82	0.297	0.528	1.21
AKIM mm.	3.25	9.84	6.58	6.02	50.6	54.9	32.5	31.0	7.32	0.794	1.41	3.14
MİL. M3	0.032	0.097	0.065	0.060	0.501	0.543	0.322	0.307	0.072	0.008	0.014	0.031

SU YILI (2006) YILLIK TOPLAM AKIM 2.05 MİLYON M3 207 MM. 6.6 LT/SN/Km2

14. Yesilırmak Havzasi

D14A104 AHİİLYAS DERESİ EVCİYENİKIŞLA

YERİ : **ÇORUM-ALACA YOL KAVŞAĞINA GELMEDEN ESKİ ANKARA YOLUNA SAPILIR 16.KM SONRA EVCIYENI KIŞLA KÖYÜNE VARILIR.İSTASYON AHŞAP KÖPRÜNÜN 10 M.MANSABINDADIR. 34°37'17" Doğu - 40°22'0" Kuzey**

YAĞIŞ ALANI : **70.00 km2** **YAKLAŞIK KOT : 1011 m**

GÖZLEM SÜRESİ : **21.11.1977 - 30.09.2006**

ORTALAMA AKIMLAR : **Gözlem süresinde 0.315 m3/sn. (15 Yıllık) 2006 Su yılında 0.220 m3/sn.**

ANLIK EN ÇOK VE EN AZ AKIMLAR:

2006 Su yılında anlık ençok akım	:	**7.70**	**m3/sn**	**10.03.2006**
2006 Su yılında anlık enaz akım	:	**0.023**	**m3/sn**	**20.12.2005**
Gözlem süresinde anlık ençok akım	:	**11.0**	**m3/sn**	**15.06.1988**
Gözlem süresinde anlık enaz akım	:	**0.000**	**m3/sn**	**14.05.1988**

İstasyon için kullanılmış anahtar bulunamadı.

Akımlar 01 Ekim 2005 'den 30 Eylül 2006' a kadar m3/sn olarak

Gün	Ekim	Kasım	Aralık	Ocak	Şubat	Mart	Nisan	Mayıs	Haziran	Temmuz	Ağustos	Eylül
01	0.050	0.050	0.035	0.023	0.035	0.285	0.365	0.590	0.127	0.050	0.035	0.035
02	0.050	0.050	0.035	0.023	0.035	0.285	0.365	0.590	0.127	0.050	0.035	0.035
03	0.050	0.050	0.035	0.023	0.035	0.760	0.365	0.470	0.127	0.050	0.035	0.035
04	0.050	0.050	0.035	0.023	0.035	0.760	0.285	0.470	0.127	0.050	0.035	0.035
05	0.069	0.050	0.035	0.023	0.035	0.940	0.285	0.470	0.127	0.050	0.035	0.035
06	0.069	0.050	0.035	0.023	0.035	1.90	0.285	0.365	0.127	0.050	0.035	0.035
07	0.069	0.050	0.035	0.023	0.035	1.90	0.365	0.365	0.094	0.050	0.035	0.035
08	0.069	0.050	0.035	0.035	0.035	1.48	0.365	0.365	0.094	0.050	0.035	0.035
09	0.069	0.050	0.035	0.035	0.035	1.48	0.365	0.365	0.094	0.050	0.035	0.035
10	0.069	0.050	0.035	0.035	0.035	2.40	0.760	0.285	0.094	0.050	0.035	0.035
11	0.069	0.050	0.035	0.023	0.035	2.40	0.760	0.285	0.094	0.050	0.035	0.035
12	0.069	0.050	0.035	0.023	0.035	1.90	0.590	0.365	0.094	0.050	0.035	0.035
13	0.069	0.050	0.035	0.023	0.069	1.90	0.590	0.365	0.094	0.050	0.035	0.035
14	0.069	0.050	0.035	0.023	0.069	1.48	0.590	0.365	0.069	0.050	0.035	0.035
15	0.069	0.050	0.035	0.023	0.050	1.48	0.470	0.285	0.069	0.050	0.035	0.035
16	0.069	0.069	0.035	0.050	0.050	1.48	0.470	0.285	0.069	0.050	0.035	0.035
17	0.069	0.069	0.035	0.035	0.094	1.90	1.13	0.285	0.050	0.050	0.035	0.035
18	0.069	0.127	0.035	0.035	0.094	1.90	1.13	0.215	0.050	0.050	0.035	0.035
19	0.069	0.094	0.035	0.035	0.069	3.00	0.940	0.215	0.050	0.050	0.035	0.035
20	0.069	0.069	0.023	0.035	0.069	2.40	0.940	0.215	0.050	0.050	0.035	0.035
21	0.069	0.050	0.023	0.035	0.069	1.48	0.760	0.215	0.050	0.050	0.035	0.035
22	0.069	0.050	0.023	0.035	0.050	1.48	0.760	0.168	0.050	0.050	0.035	0.035
23	0.050	0.050	0.023	0.035	0.050	1.13	0.760	0.168	0.050	0.050	0.035	0.035
24	0.050	0.035	0.023	0.035	0.050	1.13	0.590	0.168	0.050	0.050	0.035	0.023
25	0.050	0.035	0.023	0.023	0.050	0.940	0.365	0.168	0.050	0.050	0.035	0.023
26	0.050	0.035	0.023	0.023	0.050	0.940	0.365	0.168	0.050	0.050	0.035	0.023
27	0.050	0.035	0.023	0.023	0.127	0.940	0.365	0.127	0.050	0.050	0.035	0.023
28	0.050	0.035	0.023	0.023	0.094	0.760	0.365	0.127	0.050	0.035	0.035	0.023
29	0.050	0.035	0.023	0.023	-----	0.470	0.285	0.127	0.050	0.035	0.035	0.023
30	0.050	0.035	0.023	0.023	-----	0.470	0.285	0.127	0.050	0.035	0.035	0.023
31	0.050	-----	0.023	0.023	-----	0.470	-----	0.127	-----	0.035	0.035	-----
Maks.	0.094	0.285	0.035	0.094	0.285	7.70	2.40	0.760	0.127	0.050	0.035	0.035
Min.	0.050	0.035	0.023	0.023	0.035	0.215	0.215	0.127	0.050	0.035	0.035	0.023
Ortalama	0.061	0.052	0.030	0.028	0.054	1.36	0.544	0.287	0.078	0.048	0.035	0.032
LT/SN/Km2	0.872	0.749	0.434	0.402	0.778	19.5	7.77	4.10	1.11	0.687	0.500	0.460
AKIM mm.	2.34	1.94	1.16	1.08	1.88	52.1	20.1	11.0	2.87	1.84	1.34	1.19
MİL. M3	0.163	0.136	0.081	0.075	0.132	3.65	1.41	0.769	0.201	0.129	0.094	0.083

SU YILI (2006) YILLIK TOPLAM AKIM 6.92 MİLYON M3 99 MM. 3.1 LT/SN/Km2

14. Yesilırmak Havzasi

D14A106 ALPU D. ALPUDERE KÖYÜ

YERİ : SULUSARAY İLÇESİNE 5 KM MESAFEDEKİ ALPUDERE KÖYÜNÜN 1.5 KM. MEMBAINDADIR. 25 LİK PAFTADAKİ YERİ: H36-D4
36°5'33" Doğu - 40°3'22" Kuzey

YAĞIŞ ALANI : 70,00 km2 **YAKLAŞIK KOT** : 1095 m

GÖZLEM SÜRESİ : 20.09.1978 - 30.09.2006

ORTALAMA AKIMLAR : Gözlem süresinde 0.426 m3/sn. (27 Yıllık) 2006 Su yılında 0.152 m3/sn.

ANLIK EN ÇOK VE EN AZ AKIMLAR:

2006 Su yılında anlık ençok akım	:	1.92	m3/sn	02.04.2006
2006 Su yılında anlık enaz akım	:	0.002	m3/sn	11.09.2006
Gözlem süresinde anlık ençok akım	:	28.0	m3/sn	13.05.1998
Gözlem süresinde anlık enaz akım	:	0.000	m3/sn	03.09.1979

14. Anahtar Eğrisi (Seviyeler cm olarak)

Seviye	Akım	Seviye	Akım	Seviye	Akım	Seviye	Akım
1	0.000	20	0.900	90	12.0	160	26.0
4	0.009	25	1.4	120	18.0	170	28.0
7	0.082	37	2.8	130	20.0	180	30.0
10	0.190	44	3.9	140	22.0	200	34.0
15	0.470	60	6.4	150	24.0	250	44.0

Akımlar 01 Ekim 2005 'den 30 Eylül 2006' a kadar m3/sn olarak

Gün	Ekim	Kasım	Aralık	Ocak	Şubat	Mart	Nisan	Mayıs	Haziran	Temmuz	Ağustos	Eylül
01	0.048	0.048	0.082	0.082	0.048	0.290	0.555	0.290	0.190	0.048	0.048	0.009
02	0.048	0.048	0.082	0.082	0.048	0.290	1.59	0.720	0.190	0.048	0.048	0.009
03	0.048	0.048	0.082	0.082	0.048	0.290	1.00	0.720	0.190	0.048	0.048	0.009
04	0.048	0.048	0.082	0.082	0.048	0.290	0.720	0.555	0.190	0.048	0.048	0.009
05	0.048	0.048	0.082	0.082	0.048	0.290	0.720	0.410	0.190	0.048	0.048	0.009
06	0.048	0.048	0.082	0.082	0.048	0.240	0.640	0.410	0.150	0.048	0.048	0.009
07	0.048	0.048	0.082	0.082	0.082	0.240	0.555	0.410	0.150	0.048	0.048	0.009
08	0.048	0.048	0.048	0.082	0.150	0.240	0.555	0.410	0.150	0.048	0.024	0.009
09	0.048	0.048	0.048	0.082	0.150	0.240	0.555	0.350	0.150	0.048	0.009	0.009
10	0.048	0.048	0.048	0.082	0.190	0.240	0.410	0.350	0.240	0.048	0.009	0.009
11	0.048	0.048	0.048	0.082	0.350	0.190	0.410	0.290	0.190	0.048	0.009	0.002
12	0.048	0.048	0.048	0.082	0.290	0.190	0.410	0.290	0.150	0.048	0.009	0.002
13	0.048	0.048	0.048	0.082	0.290	0.190	0.410	0.290	0.150	0.048	0.009	0.002
14	0.048	0.048	0.082	0.082	0.290	0.190	0.350	0.290	0.150	0.048	0.024	0.002
15	0.048	0.048	0.082	0.082	0.240	0.190	0.350	0.290	0.114	0.114	0.024	0.002
16	0.048	0.048	0.082	0.082	0.190	0.190	0.350	0.410	0.114	0.114	0.009	0.002
17	0.048	0.048	0.082	0.082	0.190	0.190	0.350	0.555	0.114	0.048	0.009	0.002
18	0.048	0.048	0.082	0.082	0.190	0.190	0.290	0.410	0.114	0.082	0.009	0.002
19	0.048	0.048	0.082	0.082	0.190	0.240	0.290	0.290	0.114	0.048	0.009	0.002
20	0.048	0.048	0.082	0.150	0.240	0.290	0.290	0.290	0.082	0.048	0.009	0.002
21	0.048	0.082	0.082	0.240	0.240	0.350	0.290	0.290	0.082	0.048	0.009	0.002
22	0.048	0.082	0.082	0.240	0.190	0.410	0.290	0.290	0.048	0.048	0.009	0.024
23	0.048	0.082	0.082	0.082	0.190	0.350	0.290	0.290	0.048	0.048	0.009	0.024
24	0.048	0.082	0.082	0.082	0.240	0.350	0.290	0.290	0.048	0.048	0.009	0.009
25	0.048	0.082	0.082	0.190	0.240	0.410	0.290	0.290	0.048	0.048	0.009	0.009
26	0.048	0.082	0.048	0.082	0.240	0.470	0.290	0.240	0.048	0.048	0.009	0.009
27	0.048	0.082	0.048	0.082	0.290	0.900	0.290	0.555	0.048	0.048	0.009	0.009
28	0.048	0.082	0.048	0.082	0.290	0.720	0.290	0.470	0.048	0.048	0.009	0.009
29	0.048	0.082	0.048	0.082	-----	0.555	0.290	0.290	0.048	0.048	0.009	0.009
30	0.048	0.082	0.048	0.190	-----	0.555	0.290	0.290	0.048	0.048	0.009	0.009
31	0.048	-----	0.048	0.190	-----	0.555	-----	0.240	-----	0.048	0.009	-----
Maks.	0.048	0.082	0.082	0.290	0.900	0.900	1.92	1.29	0.290	0.114	0.048	0.024
Min.	0.048	0.048	0.024	0.082	0.048	0.190	0.290	0.190	0.048	0.048	0.009	0.002
Ortalama	0.048	0.059	0.069	0.105	0.187	0.333	0.457	0.373	0.120	0.053	0.019	0.007
LT/SN/Km2	0.686	0.848	0.983	1.50	2.67	4.76	6.52	5.33	1.71	0.762	0.275	0.106
AKIM mm.	1.84	2.20	2.63	4.01	6.47	12.7	16.9	14.3	4.44	2.04	0.737	0.275
MİL. M3	0.129	0.154	0.184	0.281	0.453	0.892	1.18	0.999	0.311	0.143	0.052	0.019

SU YILI (2006) YILLIK TOPLAM AKIM 4.80 MİLYON M3 69 MM. 2.2 LT/SN/Km2

14. Yesilırmak Havzasi

D14A112 Köse D. Köse

YERİ : **ERZİNCAN-GÜMÜŞHANE RARA YOLUNUN KÖSE NAHİYESİNDEKİ KÖPRÜNÜN 5 M. MANSABINDA SOL SAHİLDEDİR.**

39°39'0" Doğu - 40°12'30" Kuzey

YAĞIŞ ALANI : **90,69 km2** **YAKLAŞIK KOT : 1570 m**

GÖZLEM SÜRESİ : **15.06.1985 - 30.09.2006**

ORTALAMA AKIMLAR : **Gözlem süresinde 0.591 m3/sn. (18 Yıllık) 2006 Su yılında 0.590 m3/sn.**

ANLIK EN ÇOK VE EN AZ AKIMLAR:

2006 Su yılında anlık ençok akım	**:**	**5.34**	**m3/sn**	**30.04.2006**
2006 Su yılında anlık enaz akım	**:**	**0.007**	**m3/sn**	**25.08.2006**
Gözlem süresinde anlık ençok akım	**:**	**10.0**	**m3/sn**	**14.04.1988**
Gözlem süresinde anlık enaz akım	**:**	**0.000**	**m3/sn**	**01.08.1994**

Akımlar 01 Ekim 2005 'den 30 Eylül 2006' a kadar m3/sn olarak

Gün	Ekim	Kasım	Aralık	Ocak	Şubat	Mart	Nisan	Mayıs	Haziran	Temmuz	Ağustos	Eylül
01	0.014	2.95	0.176	0.080	0.051	0.304	3.45	4.54	0.336	0.208	0.051	0.007
02	0.014	1.17	0.144	0.080	0.051	0.304	3.55	4.32	0.336	0.208	0.051	0.007
03	0.014	0.400	0.144	0.080	0.051	0.304	3.15	4.43	0.336	0.208	0.051	0.007
04	0.014	0.336	0.144	0.080	0.051	0.304	2.95	4.10	0.336	0.176	0.051	0.007
05	0.014	0.336	0.144	0.080	0.051	0.336	2.75	3.55	0.336	0.176	0.051	0.007
06	0.014	0.336	0.112	0.080	0.051	0.336	2.85	3.05	0.304	0.176	0.051	0.007
07	0.014	0.368	0.112	0.112	0.051	0.620	3.35	2.75	0.304	0.144	0.051	0.007
08	0.014	0.368	0.112	0.144	0.051	0.510	3.99	3.05	0.304	0.144	0.051	0.007
09	0.014	0.368	0.112	0.112	0.066	0.620	4.21	2.95	0.304	0.144	0.037	0.007
10	0.014	0.368	0.144	0.080	0.066	0.730	4.32	2.55	0.272	0.144	0.037	0.007
11	0.014	0.336	0.144	0.080	0.066	0.730	4.32	2.45	0.240	0.144	0.037	0.007
12	0.014	0.272	0.144	0.080	0.080	0.620	3.99	2.13	0.208	0.144	0.037	0.007
13	0.014	0.240	0.144	0.080	0.080	0.620	3.55	2.13	0.208	0.144	0.022	0.007
14	0.016	0.208	0.112	0.080	0.080	0.620	3.55	1.92	0.208	0.112	0.022	0.007
15	0.052	0.176	0.080	0.080	0.080	0.730	3.15	1.71	0.208	0.112	0.022	0.007
16	0.090	0.176	0.080	0.066	0.080	0.730	2.95	1.61	0.176	0.112	0.022	0.007
17	0.090	0.144	0.080	0.066	0.080	0.730	2.45	1.50	0.176	0.080	0.022	0.007
18	0.108	0.144	0.112	0.066	0.080	0.730	2.13	1.50	0.176	0.080	0.022	0.007
19	0.210	0.144	0.080	0.066	0.066	0.730	1.92	1.28	0.176	0.080	0.037	0.007
20	0.210	0.144	0.080	0.066	0.066	0.620	1.71	0.950	0.144	0.066	0.022	0.007
21	0.210	0.144	0.080	0.066	0.080	0.620	1.61	0.840	0.144	0.066	0.022	0.008
22	0.210	0.144	0.080	0.051	0.112	0.620	1.61	0.840	0.144	0.080	0.008	0.008
23	0.210	0.080	0.080	0.066	0.112	0.620	1.82	0.840	0.144	0.080	0.008	0.008
24	0.210	0.112	0.080	0.080	0.144	0.730	4.43	0.730	0.144	0.080	0.022	0.008
25	0.210	0.112	0.080	0.080	0.176	1.71	4.10	0.620	0.144	0.080	0.008	0.008
26	0.210	0.144	0.080	0.080	0.176	1.17	3.35	0.620	0.144	0.066	0.007	0.008
27	0.210	0.144	0.080	0.080	0.240	0.950	2.95	0.620	0.272	0.066	0.007	0.008
28	0.210	0.144	0.080	0.066	0.240	1.06	2.85	0.400	0.272	0.051	0.007	0.008
29	0.210	0.144	0.080	0.066	-----	1.06	3.05	0.400	0.240	0.051	0.007	0.008
30	0.360	0.176	0.080	0.066	-----	2.03	4.77	0.400	0.208	0.051	0.007	0.008
31	2.85	-----	0.080	0.066	-----	3.25	-----	0.368	-----	0.051	0.007	-----
Maks.	3.15	3.15	0.176	0.144	0.272	3.35	5.34	4.65	0.400	0.208	0.051	0.008
Min.	0.014	0.080	0.066	0.051	0.051	0.272	1.50	0.368	0.144	0.051	0.007	0.007
Ortalama	0.195	0.344	0.106	0.078	0.092	0.808	3.16	1.91	0.231	0.114	0.028	0.007
LT/SN/Km2	2.15	3.80	1.17	0.863	1.02	8.91	34.9	21.0	2.55	1.25	0.305	0.081
AKIM mm.	5.77	9.84	3.12	2.31	2.46	23.9	90.3	56.4	6.62	3.36	0.816	0.210
MİL. M3	0.523	0.892	0.283	0.210	0.223	2.16	8.19	5.11	0.600	0.304	0.074	0.019

SU YILI (2006) YILLIK TOPLAM AKIM 18.59 MİLYON M3 205 MM. 6.5 LT/SN/Km2

14. Yesilırmak Havzasi

D14A117 ÇİLKORU D. GÖKDERE

YERİ : **TOKAT-NİKSAR YOLUNUN 3. KM SOLA SAPAN ORMAN YOLUNA GİRİLİR. 2.5 KM MESAFEDE YOL KENARINDADIR. 25 LİK PAFTADAKİ YERİ: H37-A2**
36°43'56" Doğu - 40°29'21" Kuzey

YAĞIŞ ALANI : **78,00 km2** **YAKLAŞIK KOT : 734 m**

GÖZLEM SÜRESİ : **01.10.1965 - 30.09.2006**

ORTALAMA AKIMLAR : **Gözlem süresinde 0.906 m3/sn. (38 Yıllık) 2006 Su yılında 0.535 m3/sn.**

ANLIK EN ÇOK VE EN AZ AKIMLAR:

2006 Su yılında anlık ençok akım	:	**7.96**	**m3/sn**	**13.02.2006**
2006 Su yılında anlık enaz akım	:	**0.049**	**m3/sn**	**12.08.2006**
Gözlem süresinde anlık ençok akım	:	**100.**	**m3/sn**	**03.01.1979**
Gözlem süresinde anlık enaz akım	:	**0.000**	**m3/sn**	**29.09.1999**

17. Anahtar Eğrisi (Seviyeler cm olarak)

Seviye	Akım	Seviye	Akım	Seviye	Akım	Seviye	Akım
1	0.000	11	0.170	28	1.8	90	22.0
3	0.004	13	0.265	34	3.0	120	39.0
5	0.019	15	0.380	44	5.0	160	65.0
7	0.049	17	0.520	60	9.7	180	80.0
9	0.100	23	1.1	80	17.0	200	100.

Akımlar 01 Ekim 2005 'den 30 Eylül 2006' a kadar m3/sn olarak

Gün	Ekim	Kasım	Aralık	Ocak	Şubat	Mart	Nisan	Mayıs	Haziran	Temmuz	Ağustos	Eylül
01	0.100	0.130	0.170	0.130	0.770	2.10	2.33	0.687	0.450	0.130	0.100	0.070
02	0.100	0.130	0.130	0.130	0.770	2.10	6.20	0.770	0.450	0.130	0.100	0.070
03	0.220	0.100	0.130	0.170	0.687	2.55	4.50	1.10	0.380	0.130	0.100	0.070
04	0.220	0.100	0.130	0.130	0.265	2.10	3.00	0.990	0.320	0.130	0.100	0.070
05	0.130	0.100	0.130	0.130	0.265	2.10	1.95	0.880	0.320	0.130	0.100	0.070
06	0.100	0.100	0.130	0.170	0.265	2.10	1.50	0.770	0.320	0.170	0.100	0.070
07	0.070	0.100	0.130	0.320	0.265	2.10	1.50	0.770	0.320	0.170	0.100	0.070
08	0.070	0.100	0.130	0.450	0.450	2.10	1.50	0.770	0.265	0.130	0.100	0.070
09	0.070	0.100	0.130	0.450	0.687	2.10	1.50	0.770	0.220	0.100	0.070	0.070
10	0.070	0.100	0.130	0.380	0.880	1.95	1.37	0.770	0.220	0.070	0.070	0.070
11	0.070	0.100	0.130	0.380	1.95	1.80	1.23	0.687	0.220	0.100	0.070	0.070
12	0.070	0.100	0.130	0.320	5.60	1.95	1.23	0.770	0.220	0.100	0.070	0.070
13	0.070	0.100	0.130	0.265	7.67	1.10	1.10	0.770	0.220	0.100	0.070	0.070
14	0.100	0.100	0.130	0.265	4.25	1.95	0.990	0.880	0.220	0.100	0.070	0.070
15	0.100	0.100	0.130	0.265	0.520	1.37	0.880	0.770	0.220	0.100	0.070	0.070
16	0.130	0.100	0.170	0.265	0.990	1.23	0.770	4.25	0.170	0.100	0.070	0.070
17	0.130	0.100	0.220	0.220	1.23	1.23	0.770	2.78	0.170	0.100	0.070	0.070
18	0.130	0.100	0.130	0.265	1.23	1.10	0.687	1.37	0.170	0.100	0.070	0.070
19	0.130	0.130	0.130	0.220	0.880	1.10	0.687	1.10	0.170	0.100	0.070	0.070
20	0.130	0.130	0.130	0.220	0.770	1.10	0.687	0.880	0.170	0.100	0.070	0.070
21	0.130	0.130	0.130	0.130	0.770	1.23	0.687	0.770	0.170	0.100	0.070	0.070
22	0.130	0.130	0.130	0.170	0.990	1.23	0.603	0.770	0.170	0.100	0.070	0.070
23	0.130	0.130	0.170	0.220	1.10	1.37	0.603	0.770	0.130	0.100	0.070	0.070
24	0.130	0.100	0.170	0.220	1.10	1.80	0.603	0.770	0.130	0.100	0.070	0.070
25	0.130	0.100	0.170	0.220	0.990	1.65	0.603	0.770	0.130	0.100	0.070	0.049
26	0.100	0.220	0.130	0.220	0.687	1.80	0.687	0.687	0.130	0.100	0.049	0.049
27	0.100	0.380	0.130	0.220	0.450	1.80	0.603	0.603	0.130	0.100	0.049	0.070
28	0.100	0.320	0.130	0.265	0.450	1.80	0.603	0.603	0.130	0.100	0.070	0.100
29	0.100	0.220	0.130	0.320	-----	1.80	0.603	0.520	0.130	0.100	0.070	0.100
30	0.100	0.220	0.130	0.450	-----	1.80	0.603	0.520	0.130	0.100	0.070	0.100
31	0.100	-----	0.130	0.520	-----	1.80	-----	0.520	-----	0.100	0.070	-----
Maks.	0.265	0.450	0.220	0.770	7.96	3.00	7.38	6.20	0.450	0.170	0.100	0.100
Min.	0.070	0.100	0.130	0.130	0.220	0.990	0.520	0.520	0.130	0.070	0.049	0.049
Ortalama	0.112	0.136	0.139	0.261	1.32	1.72	1.35	0.962	0.220	0.109	0.076	0.072
LT/SN/Km2	1.43	1.74	1.79	3.35	16.9	22.0	17.3	12.3	2.82	1.40	0.979	0.918
AKIM mm.	3.83	4.51	4.79	8.97	40.9	59.1	44.9	33.1	7.31	3.76	2.62	2.38
MİL. M3	0.299	0.352	0.373	0.700	3.19	4.61	3.51	2.58	0.570	0.293	0.205	0.186

SU YILI (2006) YILLIK TOPLAM AKIM 16.87 MİLYON M3 216 MM. 6.9 LT/SN/Km2

14. Yesilırmak Havzasi

D14A119 DEREKÖY D. SULUSARAY

YERİ : **TOKAT-SULUSARAY İLÇESİNDEDİR. İSTASYON 1. KM DEKİ SAĞ SAHİLDEDİR. 25 LİK PAFTADAKİ YERİ: I36-A1**
36°6'5" Doğu - 39°59'23" Kuzey

YAĞIŞ ALANI : **70,30 km2** **YAKLAŞIK KOT : 1050 m**

GÖZLEM SÜRESİ : **11.04.1987 - 30.09.2006**

ORTALAMA AKIMLAR : **Gözlem süresinde 0.315 m3/sn. (19 Yıllık) 2006 Su yılında 0.234 m3/sn.**

ANLIK EN ÇOK VE EN AZ AKIMLAR:

2006 Su yılında anlık ençok akım	**:**	**6.22**	**m3/sn**	**28.06.2006**
2006 Su yılında anlık enaz akım	**:**	**0.000**	**m3/sn**	**20.06.2006**
Gözlem süresinde anlık ençok akım	**:**	**39.6**	**m3/sn**	**25.04.2000**
Gözlem süresinde anlık enaz akım	**:**	**0.000**	**m3/sn**	**01.10.1987**

3. Anahtar Eğrisi (Seviyeler cm olarak)

Seviye	Akım	Seviye	Akım	Seviye	Akım	Seviye	Akım
1	0.000	11	0.022	24	1.2	60	12.3
3	0.000	13	0.060	26	1.5	80	21.0
5	0.000	16	0.220	28	2.0	100	30.0
7	0.001	18	0.380	35	3.6	120	38.0
9	0.005	20	0.560	50	8.6	200	70.0

Akımlar 01 Ekim 2005 'den 30 Eylül 2006' a kadar m3/sn olarak

Gün	Ekim	Kasım	Aralık	Ocak	Şubat	Mart	Nisan	Mayıs	Haziran	Temmuz	Ağustos	Eylül
01	0.011	0.105	0.150	0.150	0.105	0.380	0.460	0.560	0.460	0.005	KURU	KURU
02	0.005	0.105	0.150	0.105	0.060	0.380	0.380	0.380	0.460	0.005	KURU	KURU
03	0.022	0.060	0.105	0.105	0.060	0.380	0.560	0.460	0.460	0.002	KURU	KURU
04	0.040	0.060	0.105	0.105	0.060	0.380	0.830	0.695	0.460	0.002	KURU	KURU
05	0.040	0.105	0.105	0.105	0.105	0.380	0.830	0.695	0.460	0.001	KURU	KURU
06	0.040	0.105	0.150	0.105	0.105	0.380	1.18	0.695	0.300	0.002	KURU	KURU
07	0.040	0.105	0.150	0.150	0.105	0.380	1.18	0.695	0.300	0.002	KURU	KURU
08	0.040	0.105	0.105	0.220	0.150	0.300	1.18	0.695	0.300	0.001	KURU	KURU
09	0.022	0.105	0.105	0.220	0.220	0.380	1.18	0.695	0.380	KURU	KURU	KURU
10	0.040	0.105	0.150	0.220	0.220	0.380	0.695	0.560	0.460	0.001	KURU	KURU
11	0.040	0.105	0.150	0.220	0.220	0.300	0.560	0.560	0.460	KURU	KURU	KURU
12	0.040	0.105	0.220	0.220	0.220	0.300	0.560	0.460	0.300	KURU	KURU	KURU
13	0.040	0.105	0.220	0.220	0.220	0.300	0.560	0.560	0.220	0.001	KURU	KURU
14	0.060	0.105	0.105	0.220	0.300	0.300	0.560	0.460	0.220	KURU	KURU	KURU
15	0.060	0.060	0.150	0.220	0.220	0.300	0.560	0.460	0.105	KURU	KURU	KURU
16	0.060	0.060	0.150	0.105	0.220	0.300	0.460	1.01	0.022	KURU	KURU	KURU
17	0.060	0.105	0.150	0.060	0.300	0.300	0.460	1.50	0.011	KURU	KURU	KURU
18	0.060	0.105	0.150	0.105	0.380	0.300	0.460	1.50	0.011	KURU	KURU	KURU
19	0.060	0.150	0.105	0.150	0.380	0.300	0.380	1.50	0.011	KURU	KURU	KURU
20	0.060	0.150	0.105	0.105	0.380	0.300	0.460	1.50	0.005	0.001	KURU	KURU
21	0.060	0.105	0.150	0.105	0.220	0.300	0.460	1.50	0.005	KURU	KURU	KURU
22	0.060	0.150	0.150	0.150	0.380	0.300	0.460	1.40	0.002	KURU	KURU	0.011
23	0.060	0.150	0.150	0.220	0.380	0.300	0.460	1.40	0.001	KURU	KURU	0.011
24	0.105	0.150	0.150	0.220	0.380	0.300	0.460	1.40	0.001	KURU	KURU	0.005
25	0.105	0.150	0.150	0.150	0.380	0.150	0.560	1.40	0.001	KURU	KURU	0.150
26	0.105	0.150	0.105	0.105	0.380	0.105	0.560	1.40	0.001	KURU	KURU	0.105
27	0.105	0.150	0.150	0.105	0.380	0.380	0.560	1.70	0.001	KURU	KURU	0.022
28	0.060	0.150	0.150	0.105	0.380	0.460	0.560	1.70	0.005	KURU	KURU	0.022
29	0.060	0.150	0.150	0.150	-----	0.460	0.460	0.695	0.022	KURU	KURU	0.005
30	0.060	0.150	0.105	0.060	-----	0.460	0.560	0.560	0.011	KURU	KURU	0.150
31	0.060	-----	0.150	0.105	-----	0.460	-----	0.560	-----	KURU	KURU	-----
Maks.	0.105	0.150	0.220	0.220	0.380	0.695	1.40	3.60	6.22	0.060	0.002	3.10
Min.	0.005	0.060	0.040	0.040	0.060	0.105	0.060	0.150	KURU	KURU	KURU	KURU
Ortalama	0.054	0.115	0.140	0.148	0.247	0.335	0.620	0.947	0.182	0.001	KURU	0.016
LT/SN/Km2	0.771	1.64	1.99	2.10	3.51	4.77	8.82	13.5	2.59	0.011	0.000	0.228
AKIM mm.	2.06	4.26	5.33	5.64	8.49	12.8	22.9	36.1	6.70	0.028	0.000	0.591
MİL. M3	0.145	0.299	0.375	0.396	0.597	0.898	1.61	2.54	0.471	0.002	0.000	0.042

SU YILI (2006) YILLIK TOPLAM AKIM 7.38 MİLYON M3 105 MM. 3.3 LT/SN/Km2

14. Yesilırmak Havzasi

D14A121 KARAKUŞ Ç. KEVGİR KALESİ

YERİ : ERBAA-NİKSAR YOLUNUN 10 KM DOĞANYURT BUCAĞI İÇİNDEN AKGÜN KÖYÜNE ULAŞILIR. İSTASYON KEVGİR MAH. PATİKA YOLUNDADIR. 25 LİK PAFTADAKİ YERİ: G37-B4
36°51'1" Doğu - 40°47'15" Kuzey

YAĞIŞ ALANI : 679,00 km2 **YAKLAŞIK KOT** : 571 m

GÖZLEM SÜRESİ : 24.05.1989 - 30.09.2006

ORTALAMA AKIMLAR : Gözlem süresinde 9.214 m3/sn. (12 Yıllık) 2006 Su yılında 6.770 m3/sn.

ANLIK EN ÇOK VE EN AZ AKIMLAR:

2006 Su yılında anlık ençok akım	:	43.5	m3/sn	04.03.2006
2006 Su yılında anlık enaz akım	:	0.310	m3/sn	13.10.2005
Gözlem süresinde anlık ençok akım	:	270.	m3/sn	29.11.1989
Gözlem süresinde anlık enaz akım	:	0.000	m3/sn	20.09.1994

İstasyon için kullanılmış anahtar bulunamadı.

Akımlar 01 Ekim 2005 'den 30 Eylül 2006' a kadar m3/sn olarak

Gün	Ekim	Kasım	Aralık	Ocak	Şubat	Mart	Nisan	Mayıs	Haziran	Temmuz	Ağustos	Eylül
01	0.400	1.50	11.9	3.47	1.70	25.6	13.4	5.10	4.00	23.6	1.30	0.500
02	0.400	1.60	8.50	5.10	2.00	30.5	20.4	6.05	3.47	15.5	1.30	0.720
03	0.500	1.70	7.13	5.10	2.00	30.0	26.0	13.4	3.33	14.9	1.15	0.790
04	0.790	1.85	6.33	4.60	2.10	39.5	23.2	11.9	3.20	14.2	1.15	1.00
05	1.00	3.60	4.85	6.05	2.20	28.4	20.0	10.9	2.95	10.6	1.15	0.860
06	0.720	9.10	4.00	8.20	2.37	26.0	16.1	10.3	2.53	10.9	1.08	0.930
07	0.790	8.80	3.80	10.0	4.60	27.6	14.5	13.8	2.20	9.70	1.00	1.00
08	0.660	8.20	3.33	13.4	6.05	37.7	14.9	16.5	2.00	6.87	0.860	1.00
09	0.550	7.13	2.95	9.70	8.50	32.3	17.1	14.2	2.10	5.50	0.860	1.00
10	0.400	4.60	2.20	8.20	10.0	26.8	17.4	12.3	3.20	6.33	0.720	0.860
11	0.400	4.15	2.10	5.78	16.5	20.4	20.4	9.70	2.20	4.15	0.720	0.860
12	0.400	3.47	2.00	4.30	25.6	15.8	17.4	8.50	2.00	3.33	0.720	0.930
13	0.310	2.37	1.50	4.30	20.0	14.2	14.5	8.50	2.00	3.20	0.720	1.00
14	0.310	1.85	1.40	3.80	15.2	17.4	12.7	15.8	2.00	2.53	0.720	1.00
15	0.350	1.50	1.30	3.33	11.9	17.1	12.7	13.1	2.00	2.53	0.720	0.930
16	0.600	1.30	2.53	2.95	9.40	16.8	12.7	13.4	1.50	2.20	0.720	0.860
17	4.60	1.23	6.60	2.10	7.67	14.9	10.6	35.4	1.50	1.85	0.720	0.860
18	3.80	1.00	5.78	2.00	7.67	13.8	9.40	30.5	1.23	1.50	0.720	0.860
19	4.00	1.00	5.50	2.00	8.80	12.7	7.93	23.2	1.08	1.70	0.720	0.860
20	4.15	1.15	5.50	2.53	10.9	11.9	6.87	17.7	1.00	1.70	0.720	0.860
21	4.00	2.20	5.50	2.20	13.4	12.3	6.05	13.1	1.00	2.00	0.720	0.930
22	2.37	4.15	4.60	2.10	16.5	14.5	6.05	9.10	1.00	2.20	0.720	1.15
23	2.00	4.45	4.30	2.00	16.8	16.1	5.30	7.40	0.930	2.20	0.720	1.15
24	1.70	4.60	4.30	2.00	16.8	18.4	5.30	6.60	0.860	2.00	0.720	1.30
25	1.40	4.45	3.60	2.00	17.1	19.2	8.20	5.10	0.860	1.85	0.720	1.40
26	1.30	11.9	2.95	2.20	22.0	16.5	8.20	4.45	0.860	1.70	0.600	1.85
27	1.00	23.2	2.95	2.20	27.2	14.9	6.05	7.13	0.860	1.70	0.600	1.70
28	0.860	20.8	2.95	2.00	25.6	13.8	5.50	12.3	0.790	1.50	0.550	1.40
29	1.50	17.1	2.95	1.50	-----	13.4	5.30	8.20	1.40	1.50	0.500	1.00
30	1.85	17.7	3.47	1.50	-----	13.1	5.10	6.05	20.4	1.50	0.500	0.930
31	1.60	-----	3.60	1.50	-----	12.7	-----	4.45	-----	1.30	0.500	-----
Maks.	5.50	27.6	15.5	15.5	28.4	43.5	27.6	39.0	37.2	26.0	1.30	2.00
Min.	0.310	1.00	1.30	1.50	1.70	11.9	5.10	4.30	0.720	1.30	0.500	0.500
Ortalama	1.44	5.92	4.21	4.13	11.8	20.1	12.3	12.1	2.48	5.23	0.794	1.02
LT/SN/Km2	2.12	8.72	6.19	6.09	17.4	29.7	18.1	17.8	3.65	7.71	1.17	1.50
AKIM mm.	5.69	22.6	16.6	16.3	42.1	79.4	47.0	47.6	9.47	20.6	3.13	3.88
MİL. M3	3.86	15.3	11.3	11.1	28.6	53.9	31.9	32.3	6.43	14.0	2.13	2.63

SU YILI (2006) YILLIK TOPLAM AKIM 213.45 MİLYON M3 314 MM. 10.0 LT/SN/Km2

14. Yesilırmak Havzasi

D14A122 KARAKUŞ Ç. GÖKÇEBAYIR

YERİ : AKKUŞ-NİKSAR KARAYOLUNUN 10 KM SİNDEKİ GÖKÇEBAYIR KÖPRÜSÜNÜN 250 MANSABINDADIR.
25 LİK PAFTADAKİ YERİ: G38-D1
37°1'20" Doğu - 40°42'59" Kuzey

YAĞIŞ ALANI : 363,00 km2 **YAKLAŞIK KOT** : 905 m

GÖZLEM SÜRESİ : 25.05.1989 - 30.09.2006

ORTALAMA AKIMLAR : Gözlem süresinde 5.554 m3/sn. (13 Yıllık) 2006 Su yılında 5.106 m3/sn.

ANLIK EN ÇOK VE EN AZ AKIMLAR:

2006 Su yılında anlık ençok akım	:	67.6	m3/sn	03.03.2006
2006 Su yılında anlık enaz akım	:	0.360	m3/sn	28.08.2006
Gözlem süresinde anlık ençok akım	:	122.	m3/sn	29.03.1993
Gözlem süresinde anlık enaz akım	:	0.022	m3/sn	01.09.2003

2. Anahtar Eğrisi (Seviyeler cm olarak)

Seviye	Akım	Seviye	Akım	Seviye	Akım	Seviye	Akım
39	0.000	64	0.200	89	2.2	240	51.0
44	0.017	69	0.330	94	2.8	290	84.0
49	0.035	74	0.560	99	3.7		
54	0.060	79	0.950	140	14.0		
59	0.115	84	1.5	190	30.0		

Akımlar 01 Ekim 2005 'den 30 Eylül 2006' a kadar m3/sn olarak

Gün	Ekim	Kasım	Aralık	Ocak	Şubat	Mart	Nisan	Mayıs	Haziran	Temmuz	Ağustos	Eylül
01	1.40	3.44	9.70	2.74	1.76	29.5	9.48	3.72	3.02	8.04	0.895	0.360
02	1.52	3.30	7.20	3.30	1.64	29.1	17.6	5.15	2.60	8.04	0.730	0.460
03	1.40	3.30	5.80	3.44	1.52	35.4	21.2	9.92	2.24	8.04	0.665	0.530
04	1.52	3.30	5.15	3.30	1.40	41.0	17.6	8.04	2.00	4.38	0.665	0.600
05	1.40	4.25	4.25	3.16	1.52	25.9	15.2	7.48	1.88	3.44	0.600	0.600
06	1.15	9.04	3.58	4.25	1.52	26.4	12.4	8.82	1.76	5.37	0.530	0.530
07	0.978	8.32	3.02	7.48	2.60	32.2	10.6	9.92	1.76	4.50	0.530	0.665
08	0.978	8.82	2.36	6.36	2.74	45.0	11.8	13.7	1.76	3.58	0.530	0.600
09	0.978	7.76	2.12	4.50	4.25	32.7	12.4	10.6	1.64	2.88	0.530	0.600
10	0.978	5.58	2.00	3.86	3.86	19.4	11.4	9.48	1.76	2.36	0.530	0.600
11	0.978	3.72	2.00	3.30	9.70	12.4	15.6	7.20	1.64	2.00	0.530	0.600
12	0.978	2.48	2.00	3.02	21.2	10.1	11.4	5.58	1.64	1.76	0.530	0.665
13	0.978	2.24	1.76	2.74	13.4	10.4	9.70	5.80	1.64	1.76	0.530	0.813
14	0.978	2.12	1.52	2.48	9.04	16.8	8.60	8.82	1.52	1.64	0.530	0.730
15	0.978	2.12	1.64	2.24	6.92	19.4	9.04	7.20	1.52	1.40	0.410	0.600
16	1.15	2.12	4.25	1.88	5.15	11.8	8.32	6.08	1.40	1.32	0.410	0.600
17	3.86	1.76	5.37	1.76	4.25	9.48	6.36	35.8	1.32	1.15	0.410	0.600
18	2.48	1.64	4.38	1.88	4.25	7.76	4.93	23.6	1.32	1.15	0.410	0.530
19	3.72	1.64	4.50	1.88	4.50	7.48	4.50	16.8	1.23	1.15	0.410	0.530
20	3.30	1.64	4.50	2.00	5.58	7.20	4.25	10.8	1.15	1.15	0.410	0.530
21	2.88	2.36	4.38	1.64	5.37	6.92	4.13	8.60	1.15	1.32	0.460	0.530
22	2.36	2.74	3.86	1.76	5.80	7.76	3.72	6.64	0.978	1.40	0.530	0.665
23	2.24	2.74	3.58	2.00	6.64	9.92	3.44	5.15	0.895	1.40	0.460	0.813
24	2.60	3.16	3.44	2.00	7.48	13.0	3.44	4.25	0.895	1.32	0.410	1.23
25	2.74	3.16	3.02	2.00	9.70	16.0	6.64	3.58	0.895	1.23	0.410	1.64
26	2.74	6.64	3.02	2.00	13.4	10.6	4.72	3.30	0.895	1.23	0.410	2.36
27	2.74	15.6	3.16	1.76	20.5	9.70	4.00	6.36	0.895	1.23	0.410	1.88
28	2.74	16.0	3.16	1.76	19.8	10.6	3.58	8.04	0.895	1.15	0.360	1.32
29	3.86	11.1	3.02	1.76	-----	9.48	3.30	4.93	0.978	1.15	0.360	0.978
30	3.72	16.0	2.60	1.76	-----	9.04	3.72	4.00	7.48	1.06	0.360	0.813
31	3.72	-----	2.48	1.76	-----	10.4	-----	3.44	-----	0.978	0.360	-----
Maks.	4.72	23.3	12.1	8.04	25.0	67.6	22.6	52.6	34.7	18.7	0.895	2.48
Min.	0.895	1.64	1.52	1.64	1.32	6.64	3.16	2.88	0.730	0.895	0.360	0.360
Ortalama	2.07	5.27	3.64	2.77	6.98	17.5	8.77	8.80	1.69	2.53	0.494	0.799
LT/SN/Km2	5.69	14.5	10.0	7.62	19.2	48.2	24.2	24.2	4.66	6.98	1.36	2.20
AKIM mm.	15.2	37.6	26.9	20.4	46.5	129.	62.6	64.9	12.1	18.7	3.65	5.71
MİL. M3	5.53	13.7	9.75	7.41	16.9	46.9	22.7	23.6	4.39	6.79	1.32	2.07

SU YILI (2006) YILLIK TOPLAM AKIM 161.06 MİLYON M3 444 MM. 14.1 LT/SN/Km2

14. Yesilırmak Havzasi

D14A125 TERSUN D. DİLEKYOLU

YERİ : **ŞİRAN - TRABZON YOLUNUN 13. KM SİNDE DİLAK KÖYÜ YOLUNDA SOL SAHİLDEDİR.**
39°17'0" Doğu - 40°13'30" Kuzey

YAĞIŞ ALANI : **36,70 km2** **YAKLAŞIK KOT : 1610 m**

GÖZLEM SÜRESİ : **01.10.1988 – 30.09.2006**

ORTALAMA AKIMLAR : **Gözlem süresinde 0.315 m3/sn. (6 Yıllık) 2006 Su yılında 0.315 m3/sn.**

ANLIK EN ÇOK VE EN AZ AKIMLAR:

2006 Su yılında anlık ençok akım	:	**5.30**	**m3/sn**	**30.04.2006**
2006 Su yılında anlık enaz akım	:	**0.000**	**m3/sn**	**01.08.2006**
Gözlem süresinde anlık ençok akım	:	**5.86**	**m3/sn**	**06.03.2004**
Gözlem süresinde anlık enaz akım	:	**0.000**	**m3/sn**	**22.08.1999**

Akımlar 01 Ekim 2005 'den 30 Eylül 2006' a kadar m3/sn olarak

Gün	Ekim	Kasım	Aralık	Ocak	Şubat	Mart	Nisan	Mayıs	Haziran	Temmuz	Ağustos	Eylül
01	0.013	0.327	0.154	0.071	0.071	0.373	1.35	2.90	0.208	0.028	KURU	KURU
02	0.010	0.235	0.127	0.071	0.071	0.373	1.45	3.34	0.181	0.020	KURU	KURU
03	0.010	0.208	0.127	0.071	0.071	0.419	1.45	3.63	0.154	0.020	KURU	KURU
04	0.010	0.208	0.154	0.071	0.071	0.465	1.15	2.62	0.154	0.013	KURU	KURU
05	0.013	0.235	0.127	0.071	0.071	0.465	1.05	2.07	0.127	0.010	KURU	KURU
06	0.013	0.235	0.127	0.071	0.071	0.517	0.920	2.07	0.100	0.013	KURU	KURU
07	0.010	0.208	0.100	0.071	0.071	0.673	0.855	1.81	0.100	0.020	KURU	KURU
08	0.013	0.208	0.086	0.071	0.071	0.855	0.920	2.20	0.100	0.042	KURU	KURU
09	0.013	0.208	0.086	0.071	0.071	0.790	1.45	1.94	0.100	0.020	KURU	KURU
10	0.013	0.181	0.071	0.071	0.071	0.621	1.45	1.55	0.071	0.013	KURU	KURU
11	0.013	0.154	0.071	0.071	0.071	0.465	1.81	1.25	0.042	0.010	KURU	KURU
12	0.010	0.127	0.086	0.071	0.071	0.465	1.94	0.985	0.057	0.010	KURU	KURU
13	0.010	0.100	0.154	0.071	0.071	0.465	1.55	0.920	0.057	0.010	KURU	KURU
14	0.013	0.086	0.181	0.071	0.086	0.569	1.25	0.855	0.042	0.005	KURU	KURU
15	0.028	0.086	0.057	0.071	0.208	0.673	1.25	0.790	0.042	0.003	KURU	KURU
16	0.042	0.071	0.071	0.071	0.569	0.621	1.05	0.673	0.042	0.005	KURU	KURU
17	0.235	0.057	0.071	0.071	0.373	0.569	0.920	0.621	0.028	0.005	KURU	KURU
18	0.086	0.057	0.071	0.071	0.154	0.569	0.790	0.621	0.028	0.005	KURU	KURU
19	0.100	0.057	0.071	0.071	0.127	0.517	0.725	0.569	0.020	0.003	KURU	KURU
20	0.154	0.057	0.071	0.071	0.419	0.517	0.725	0.465	0.020	0.005	KURU	KURU
21	0.100	0.071	0.071	0.071	0.465	0.465	0.673	0.465	0.020	0.003	KURU	KURU
22	0.086	0.071	0.154	0.071	0.621	0.569	0.673	0.465	0.020	0.003	KURU	KURU
23	0.071	0.086	0.071	0.071	0.569	0.621	0.725	0.419	0.010	0.003	KURU	0.001
24	0.057	0.100	0.154	0.071	0.517	0.673	2.20	0.373	0.013	0.003	KURU	0.003
25	0.042	0.086	0.127	0.071	0.208	1.25	1.94	0.327	0.020	0.003	KURU	0.003
26	0.042	0.086	0.127	0.071	0.281	1.35	1.55	0.327	0.013	0.002	KURU	0.003
27	0.042	0.100	0.071	0.071	0.327	1.05	1.25	0.327	0.010	0.002	KURU	0.003
28	0.071	0.127	0.071	0.071	0.373	0.920	1.05	0.327	0.010	0.001	KURU	0.003
29	0.127	0.154	0.071	0.071	-----	0.920	1.05	0.281	0.086	0.001	KURU	0.005
30	0.154	0.154	0.071	0.071	-----	0.920	3.48	0.235	0.042	0.001	KURU	0.005
31	0.419	-----	0.071	0.071	-----	1.05	-----	0.208	-----	0.001	KURU	-----
Maks.	0.592	0.320	0.400	0.060	1.97	1.68	5.30	4.44	0.177	0.048	KURU	0.007
Min.	0.011	0.048	0.048	0.060	0.060	0.280	0.592	0.177	0.007	0.001	KURU	KURU
Ortalama	0.065	0.138	0.101	0.071	0.222	0.670	1.29	1.15	0.064	0.009	KURU	0.001
LT/SN/Km2	1.78	3.76	2.74	1.93	6.05	18.3	35.1	31.3	1.74	0.249	0.000	0.024
AKIM mm.	4.76	9.75	7.35	5.18	14.6	48.9	91.0	83.9	4.51	0.666	0.000	0.061
MİL. M3	0.175	0.358	0.270	0.190	0.537	1.79	3.34	3.08	0.166	0.024	0.000	0.002

SU YILI (2006) YILLIK TOPLAM AKIM 9.93 MİLYON M3 271 MM. 8.6 LT/SN/Km2

14. Yesilırmak Havzasi

D14A126 CEVİZLİK D. ERENKAYA

YERİ : **GÜMÜŞHANENİN ŞİRAN İLÇESİNİN ULUŞİRAN KÖYÜNÜN 500M ÇIKIŞINDA SAĞ SAHİLDEDİR.**
39°6'30" Doğu - 40°14'0" Kuzey

YAĞIŞ ALANI : **21,96 km2** **YAKLAŞIK KOT : 1500 m**

GÖZLEM SÜRESİ : **01.10.1989 - 30.09.2006**

ORTALAMA AKIMLAR : **Gözlem süresinde 0.328 m3/sn. (15 Yıllık) 2006 Su yılında 0.390 m3/sn.**

ANLIK EN ÇOK VE EN AZ AKIMLAR:

2006 Su yılında anlık ençok akım	:	**4.54**	**m3/sn**	**06.05.2006**
2006 Su yılında anlık enaz akım	:	**0.004**	**m3/sn**	**01.10.2005**
Gözlem süresinde anlık ençok akım	:	**5.20**	**m3/sn**	**25.04.2003**
Gözlem süresinde anlık enaz akım	:	**0.001**	**m3/sn**	**10.02.1990**

Akımlar 01 Ekim 2005 'den 30 Eylül 2006' a kadar m3/sn olarak

Gün	Ekim	Kasım	Aralık	Ocak	Şubat	Mart	Nisan	Mayıs	Haziran	Temmuz	Ağustos	Eylül
01	0.004	0.020	0.038	0.038	0.012	0.020	0.074	4.06	0.210	0.420	0.420	0.183
02	0.005	0.020	0.038	0.029	0.012	0.020	0.133	3.74	0.210	0.380	0.340	0.155
03	0.008	0.016	0.029	0.020	0.016	0.029	0.110	3.98	0.210	0.270	0.305	0.155
04	0.008	0.012	0.020	0.029	0.016	0.029	0.074	4.22	0.155	0.183	0.270	0.133
05	0.012	0.012	0.038	0.029	0.012	0.049	0.074	4.14	0.155	0.210	0.240	0.110
06	0.016	0.020	0.038	0.029	0.016	0.060	0.110	4.30	0.110	0.270	0.210	0.155
07	0.020	0.020	0.029	0.038	0.016	0.049	0.090	4.46	0.155	0.183	0.270	0.155
08	0.029	0.020	0.029	0.020	0.016	0.049	0.074	4.38	0.210	0.155	0.270	0.270
09	0.016	0.029	0.020	0.016	0.012	0.049	0.155	4.30	0.240	0.133	0.270	0.270
10	0.016	0.029	0.012	0.016	0.012	0.029	0.183	4.22	0.270	0.155	0.305	0.240
11	0.110	0.020	0.005	0.038	0.008	0.029	0.155	3.98	0.240	0.270	0.340	0.210
12	0.380	0.016	0.005	0.038	0.008	0.020	0.074	3.90	0.210	0.240	0.305	0.210
13	0.380	0.020	0.008	0.038	0.005	0.016	0.074	3.74	0.240	0.210	0.270	0.210
14	0.049	0.029	0.012	0.049	0.012	0.029	0.110	3.26	0.270	0.210	0.270	0.110
15	0.029	0.029	0.016	0.038	0.016	0.016	0.090	2.94	0.340	0.183	0.270	0.110
16	0.074	0.029	0.020	0.029	0.016	0.016	0.690	2.78	0.380	0.240	0.240	0.090
17	0.060	0.038	0.038	0.020	0.020	0.029	1.70	2.30	0.270	0.210	0.340	0.074
18	0.074	0.049	0.038	0.029	0.020	0.029	1.42	2.15	0.240	0.270	0.474	0.060
19	0.049	0.060	0.049	0.038	0.020	0.029	1.22	2.08	0.210	0.270	0.732	0.049
20	0.020	0.060	0.060	0.038	0.029	0.020	1.29	1.55	0.183	0.340	0.732	0.038
21	0.012	0.038	0.049	0.038	0.029	0.016	1.16	1.22	0.155	0.340	0.690	0.038
22	0.008	0.020	0.038	0.029	0.020	0.016	1.16	0.774	0.210	0.380	0.636	0.029
23	0.012	0.016	0.060	0.016	0.020	0.016	1.16	0.732	0.270	0.528	0.582	0.029
24	0.012	0.012	0.074	0.016	0.029	0.029	2.00	0.582	0.340	0.636	0.528	0.029
25	0.008	0.008	0.090	0.020	0.016	0.074	2.23	0.420	0.340	0.528	0.528	0.016
26	0.005	0.020	0.090	0.016	0.012	0.183	1.85	0.380	0.380	0.528	0.270	0.012
27	0.012	0.020	0.060	0.016	0.016	0.155	1.55	0.340	0.340	0.528	0.270	0.016
28	0.016	0.038	0.060	0.012	0.012	0.090	1.35	0.420	0.816	0.528	0.270	0.016
29	0.038	0.060	0.049	0.016	-----	0.049	1.93	0.474	0.964	0.420	0.270	0.029
30	0.060	0.038	0.038	0.016	-----	0.060	3.66	0.305	0.380	0.420	0.240	0.049
31	0.074	-----	0.060	0.012	-----	0.090	-----	0.270	-----	0.528	0.270	-----
Maks.	0.528	0.060	0.110	0.060	0.029	0.183	3.90	4.54	1.42	0.732	0.900	0.305
Min.	0.004	0.005	0.005	0.012	0.005	0.016	0.060	0.270	0.110	0.090	0.210	0.008
Ortalama	0.052	0.027	0.039	0.027	0.016	0.045	0.865	2.46	0.290	0.328	0.369	0.108
LT/SN/Km2	2.37	1.24	1.78	1.21	0.729	2.05	39.4	112.	13.2	14.9	16.8	4.93
AKIM mm.	6.36	3.22	4.76	3.25	1.76	5.48	102.	301.	34.2	40.0	45.0	12.8
MİL. M3	0.140	0.071	0.105	0.071	0.039	0.120	2.24	6.60	0.752	0.878	0.987	0.281

SU YILI (2006) YILLIK TOPLAM AKIM 12.28 MİLYON M3 559 MM. 17.7 LT/SN/Km2

14. Yesilırmak Havzasi

D14A127 ULUŞİRAN D. ERENKAYA

YERİ : **GÜMÜŞHANENİN ŞİRAN İLÇESİNİN ULUŞİRAN KÖYÜNÜN İÇERİSİNDE SAĞ SAHİLDEDİR.**
39°6'30" Doğu - 40°14'0" Kuzey

YAĞIŞ ALANI : **89,42 km2** **YAKLAŞIK KOT : 1497 m**

GÖZLEM SÜRESİ : **01.10.1988 - 30.09.2006**

ORTALAMA AKIMLAR : **Gözlem süresinde 1.332 m3/sn. (15 Yıllık) 2006 Su yılında 1.345 m3/sn.**

ANLIK EN ÇOK VE EN AZ AKIMLAR:

2006 Su yılında anlık ençok akım	:	**23.3**	**m3/sn**	**30.04.2006**
2006 Su yılında anlık enaz akım	:	**0.011**	**m3/sn**	**16.08.2006**
Gözlem süresinde anlık ençok akım	:	**31.0**	**m3/sn**	**26.04.2003**
Gözlem süresinde anlık enaz akım	:	**0.000**	**m3/sn**	**29.08.1997**

Akımlar 01 Ekim 2005 'den 30 Eylül 2006' a kadar m3/sn olarak

Gün	Ekim	Kasım	Aralık	Ocak	Şubat	Mart	Nisan	Mayıs	Haziran	Temmuz	Ağustos	Eylül
01	0.250	0.819	0.468	0.206	0.182	0.510	3.48	13.2	4.63	1.29	0.073	0.037
02	0.225	0.660	0.468	0.149	0.182	0.560	3.65	13.2	4.84	1.11	0.064	0.055
03	0.200	0.610	0.426	0.133	0.182	0.710	2.95	12.3	4.42	0.819	0.064	0.064
04	0.200	0.560	0.384	0.116	0.166	0.878	2.43	9.24	3.83	0.610	0.064	0.064
05	0.200	0.468	0.300	0.149	0.166	0.996	2.07	8.85	3.65	0.660	0.064	0.064
06	0.160	0.426	0.276	0.166	0.166	1.17	1.89	8.85	3.13	0.560	0.073	0.064
07	0.160	0.426	0.253	0.206	0.182	1.29	2.60	8.58	2.60	0.468	0.064	0.073
08	0.160	0.384	0.276	0.206	0.206	1.23	3.13	5.89	2.43	0.468	0.055	0.082
09	0.140	0.300	0.253	0.206	0.206	1.11	4.21	5.05	2.25	0.468	0.048	0.082
10	0.200	0.300	0.206	0.166	0.182	1.06	5.26	5.89	1.98	0.342	0.028	0.082
11	0.225	0.276	0.206	0.166	0.166	0.996	5.26	7.20	1.62	0.276	0.028	0.064
12	0.180	0.253	0.206	0.182	0.166	0.996	8.03	7.20	1.89	0.300	0.028	0.064
13	0.160	0.342	0.253	0.206	0.166	0.937	6.93	6.10	1.71	0.166	0.022	0.064
14	0.160	0.426	0.253	0.206	0.182	0.878	7.48	5.89	1.23	0.133	0.018	0.048
15	0.353	0.468	0.253	0.229	0.206	0.878	8.03	4.84	1.11	0.116	0.014	0.048
16	0.550	0.468	0.229	0.229	0.206	0.710	7.20	3.48	0.996	0.100	0.011	0.043
17	0.730	0.426	0.206	0.206	0.206	0.996	7.20	3.30	0.937	0.100	0.022	0.055
18	0.670	0.426	0.206	0.182	0.229	1.11	5.89	2.43	0.878	0.082	0.028	0.064
19	0.550	0.342	0.206	0.182	0.253	1.11	5.68	2.16	0.760	0.082	0.055	0.073
20	0.508	0.300	0.182	0.166	0.253	1.23	5.47	1.89	0.710	0.082	0.055	0.073
21	0.385	0.300	0.229	0.206	0.276	1.23	4.84	1.89	0.660	0.064	0.037	0.100
22	0.353	0.384	0.253	0.182	0.300	1.23	4.84	1.71	0.710	0.064	0.032	0.100
23	0.250	0.384	0.253	0.166	0.426	1.29	6.10	1.71	0.660	0.064	0.048	0.100
24	0.250	0.384	0.253	0.166	0.468	1.35	12.7	1.62	0.560	0.064	0.055	0.082
25	0.250	0.384	0.300	0.166	0.468	1.62	10.8	1.53	0.560	0.082	0.064	0.082
26	0.250	0.300	0.342	0.182	0.426	1.71	7.20	1.62	0.560	0.082	0.064	0.082
27	0.353	0.342	0.342	0.206	0.384	1.62	5.47	1.71	0.426	0.082	0.073	0.082
28	0.425	0.384	0.468	0.166	0.384	1.71	5.05	1.98	1.44	0.064	0.082	0.082
29	0.790	0.560	0.253	0.206	-----	2.25	6.93	1.89	3.48	0.064	0.064	0.091
30	1.25	0.510	0.276	0.206	-----	2.95	15.9	2.07	1.35	0.082	0.055	0.100
31	1.25	-----	0.300	0.206	-----	3.13	-----	5.05	-----	0.082	0.048	-----
Maks.	1.49	0.878	0.468	0.253	0.510	3.30	23.3	14.5	5.05	1.89	0.133	0.100
Min.	0.123	0.253	0.182	0.100	0.149	0.468	1.71	1.53	0.426	0.055	0.011	0.037
Ortalama	0.380	0.420	0.283	0.184	0.249	1.27	5.96	5.11	1.87	0.291	0.048	0.072
LT/SN/Km2	4.25	4.70	3.17	2.06	2.79	14.2	66.6	57.1	20.9	3.26	0.541	0.807
AKIM mm.	11.4	12.2	8.48	5.52	6.75	38.1	173.	153.	54.1	8.72	1.45	2.09
MİL. M3	1.02	1.09	0.759	0.494	0.604	3.41	15.4	13.7	4.84	0.780	0.130	0.187

SU YILI (2006) YILLIK TOPLAM AKIM 42.41 MİLYON M3 474 MM. 15.0 LT/SN/Km2

14. Yesilırmak Havzasi

D14A133 KANLI D. PAMUKLU

YERİ : **SAMSUN-AMASYA KARAYOLUNUN AMASYAYA 10 KM MESAFESİNDEKİ DEĞİRMENDERE KÖYÜNE AYRILAN YOLUN 4 KM PAMUKLU MAHALLESİNDEKİ KÖPRÜDEDİR. 25 LİK PAFTADAKİ YERİ: G35-B4 35°48'20" Doğu - 40°46'14" Kuzey**

YAĞIŞ ALANI : **45,30 km2** **YAKLAŞIK KOT : 600 m**

GÖZLEM SÜRESİ : **02.11.1994 - 30.09.2006**

ORTALAMA AKIMLAR : **Gözlem süresinde 0.289 m3/sn. (11 Yıllık) 2006 Su yılında 0.221 m3/sn.**

ANLIK EN ÇOK VE EN AZ AKIMLAR:

2006 Su yılında anlık ençok akım	**:**	**4.40**	**m3/sn**	**17.03.2006**
2006 Su yılında anlık enaz akım	**:**	**0.000**	**m3/sn**	**18.08.2006**
Gözlem süresinde anlık ençok akım	**:**	**23.0**	**m3/sn**	**21.05.2005**
Gözlem süresinde anlık enaz akım	**:**	**0.000**	**m3/sn**	**01.07.2001**

İstasyon için kullanılmış anahtar bulunamadı.

Akımlar 01 Ekim 2005 'den 30 Eylül 2006' a kadar m3/sn olarak

Gün	Ekim	Kasım	Aralık	Ocak	Şubat	Mart	Nisan	Mayıs	Haziran	Temmuz	Ağustos	Eylül
01	0.018	0.170	0.170	0.170	1.57	0.430	0.660	0.220	0.090	0.310	0.006	0.001
02	0.018	0.170	0.170	0.170	0.100	0.545	0.660	0.220	0.090	0.220	0.006	0.001
03	0.027	0.170	0.170	0.170	0.100	0.660	0.660	0.220	0.090	0.220	0.006	0.002
04	0.050	0.170	0.170	0.170	0.050	0.660	0.660	0.220	0.090	0.220	0.009	KURU
05	0.018	0.430	0.170	0.170	0.050	0.660	0.430	0.220	0.069	0.220	0.006	KURU
06	0.008	0.430	0.170	0.170	0.100	0.660	0.430	0.220	0.052	0.090	0.006	KURU
07	0.008	0.430	0.170	0.170	0.100	0.660	0.430	0.220	0.052	0.024	0.002	KURU
08	0.008	0.430	0.170	0.170	0.050	0.660	0.430	0.220	0.052	0.024	0.002	0.001
09	0.008	0.430	0.170	0.170	0.027	1.00	0.430	0.220	0.052	0.024	0.006	0.002
10	0.008	0.430	0.170	0.170	0.050	0.660	0.430	0.220	0.052	0.009	0.006	0.002
11	0.008	0.430	0.170	0.170	0.027	0.660	0.545	0.220	0.052	0.006	0.009	0.002
12	0.008	0.430	0.170	0.170	0.100	0.430	0.855	0.220	0.052	0.006	0.002	0.002
13	0.008	0.430	0.170	0.170	0.100	0.430	0.695	0.220	0.052	0.006	0.002	0.006
14	0.008	0.430	0.100	0.170	0.050	0.170	0.695	0.265	0.069	0.015	0.001	0.006
15	0.008	0.430	0.100	0.170	0.050	0.170	0.695	0.310	0.090	0.009	0.002	0.006
16	0.050	0.430	0.100	0.170	0.050	0.320	0.553	0.265	0.069	0.009	0.009	0.006
17	0.050	0.430	0.100	0.100	0.027	1.10	0.553	0.487	0.052	0.015	0.009	0.006
18	0.050	0.430	0.100	0.100	0.018	0.760	0.553	0.487	0.037	0.009	KURU	0.002
19	0.050	0.430	0.100	0.100	0.018	0.760	0.553	0.310	0.024	0.006	KURU	KURU
20	0.050	0.800	0.170	0.100	0.050	0.760	0.420	0.310	0.024	0.006	KURU	KURU
21	0.050	0.430	0.100	0.100	0.100	0.760	0.420	0.265	0.024	0.006	0.002	0.002
22	0.050	0.320	0.170	0.100	0.100	0.760	0.420	0.220	0.024	0.006	0.002	0.037
23	0.050	0.170	0.170	0.100	0.170	0.840	0.420	0.180	0.024	0.006	0.002	0.069
24	0.050	0.100	0.170	0.100	0.320	1.34	0.420	0.180	0.024	0.006	0.001	0.069
25	0.050	0.170	0.170	0.100	0.320	1.10	0.310	0.220	0.024	0.006	KURU	0.052
26	0.100	0.170	0.170	0.100	0.430	0.920	0.310	0.265	0.024	0.009	KURU	0.069
27	0.170	0.170	0.170	0.050	0.545	0.920	0.310	0.487	0.024	0.009	KURU	0.037
28	0.170	0.170	0.170	0.100	0.545	1.01	0.310	0.420	0.024	0.009	KURU	0.052
29	0.170	0.170	0.170	0.170	-----	1.22	0.265	0.310	0.037	0.009	KURU	0.037
30	0.170	0.170	0.170	2.34	-----	1.34	0.265	0.145	0.365	0.006	KURU	0.037
31	0.170	-----	0.170	2.65	-----	1.01	-----	0.090	-----	0.006	KURU	-----
Maks.	0.170	1.00	0.320	3.40	1.57	4.40	1.30	0.553	0.420	0.310	0.024	0.115
Min.	0.004	0.050	0.100	0.027	0.011	0.170	0.265	0.090	0.024	0.006	KURU	KURU
Ortalama	0.054	0.332	0.154	0.291	0.186	0.754	0.493	0.261	0.060	0.049	0.003	0.017
LT/SN/Km2	1.18	7.34	3.40	6.43	4.11	16.6	10.9	5.75	1.33	1.09	0.068	0.372
AKIM mm.	3.17	19.0	9.12	17.2	9.95	44.6	28.2	15.4	3.44	2.91	0.183	0.965
MİL. M3	0.144	0.861	0.413	0.780	0.451	2.02	1.28	0.698	0.156	0.132	0.008	0.044

SU YILI (2006) YILLIK TOPLAM AKIM 6.99 MİLYON M3 154 MM. 4.9 LT/SN/Km2

14. Yesilırmak Havzasi

D14A135 ALACA ÇAYI DEREYAZICI

YERİ : **ÇORUM-ORTAKÖY YOLUNUN 26. KM. SİNDEN SAĞA DÖNÜLEREK 15. KM. SONRA DEREYAZICI KÖYÜNE VARILIR. KÖY İÇİNDEKİ KÖPRÜNÜN 15 M. MANSABINDA SAĞ SAHİLİNDEDİR. 34°57'43" Doğu - 40°16'40" Kuzey**

YAĞIŞ ALANI : **156.40 km2** **YAKLAŞIK KOT : 768 m**

GÖZLEM SÜRESİ : **01.10.1994 - 30.09.2006**

ORTALAMA AKIMLAR : **Gözlem süresinde 1.344 m3/sn. (4 Yıllık) 2006 Su yılında 1.810 m3/sn.**

ANLIK EN ÇOK VE EN AZ AKIMLAR:

2006 Su yılında anlık ençok akım	**:**	**19.0**	**m3/sn**	**26.03.2006**
2006 Su yılında anlık enaz akım	**:**	**0.046**	**m3/sn**	**07.08.2006**
Gözlem süresinde anlık ençok akım	**:**	**19.0**	**m3/sn**	**26.03.2006**
Gözlem süresinde anlık enaz akım	**:**	**0.014**	**m3/sn**	**26.07.2001**

İstasyon için kullanılmış anahtar bulunamadı.

Akımlar 01 Ekim 2005 'den 30 Eylül 2006' a kadar m3/sn olarak

Gün	Ekim	Kasım	Aralık	Ocak	Şubat	Mart	Nisan	Mayıs	Haziran	Temmuz	Ağustos	Eylül
01	0.102	0.170	0.474	0.520	0.788	6.00	13.3	3.15	0.587	1.37	0.121	0.084
02	0.102	0.170	0.520	0.520	0.788	7.00	12.9	2.70	0.587	1.28	0.121	0.230
03	0.102	0.170	0.520	0.520	0.654	6.25	12.9	3.00	0.520	1.06	0.102	0.230
04	0.121	0.230	0.520	0.520	0.520	7.25	13.3	3.00	0.520	0.993	0.084	0.230
05	0.121	0.260	0.520	0.520	0.520	5.82	9.70	3.00	0.587	0.924	0.084	0.170
06	0.121	0.260	0.520	0.520	0.587	5.10	7.75	3.00	0.520	0.855	0.084	0.140
07	0.121	0.260	0.520	0.520	0.721	4.74	7.00	3.00	0.474	0.855	0.046	0.170
08	0.121	0.260	0.520	0.520	1.06	4.56	6.50	3.00	0.474	0.855	0.046	0.170
09	0.121	0.260	0.520	0.520	1.45	4.56	6.25	3.00	0.474	0.855	0.065	0.140
10	0.121	0.260	0.520	0.520	1.37	4.20	5.64	3.00	0.474	1.06	0.084	0.140
11	0.121	0.260	0.474	0.520	2.15	3.90	5.46	3.00	0.474	0.924	0.084	0.140
12	0.121	0.260	0.474	0.520	5.82	3.75	5.46	2.85	0.788	0.924	0.102	0.140
13	0.121	0.260	0.474	0.520	4.74	3.60	5.46	2.59	0.788	0.924	0.102	0.140
14	0.121	0.290	0.474	0.520	3.75	3.45	5.46	2.59	0.721	0.855	0.102	0.170
15	0.121	0.290	0.474	0.520	3.15	3.75	5.10	2.48	0.721	0.587	0.102	0.140
16	0.121	0.336	0.520	0.520	3.15	3.75	5.10	2.26	0.721	0.587	0.121	0.140
17	0.140	0.336	0.520	0.520	3.15	3.90	5.10	2.26	0.721	0.587	0.121	0.140
18	0.140	0.336	0.428	0.520	2.70	4.05	5.10	2.26	0.587	0.474	0.121	0.140
19	0.140	0.336	0.382	0.520	2.70	4.92	4.20	1.62	0.520	0.474	0.121	0.140
20	0.170	0.336	0.428	0.788	3.15	6.25	4.20	1.62	0.520	0.382	0.121	0.140
21	0.170	1.20	0.474	0.788	3.30	8.25	4.20	1.45	0.788	0.230	0.121	0.170
22	0.170	1.28	0.474	0.788	3.45	10.0	4.20	1.45	0.993	0.170	0.121	0.474
23	0.170	0.924	0.520	0.788	3.45	10.0	3.60	1.13	0.993	0.200	0.084	0.290
24	0.170	0.654	0.520	0.855	3.75	10.0	3.60	1.13	0.924	0.170	0.084	0.474
25	0.170	0.587	0.520	0.855	4.20	12.6	3.30	0.924	0.654	0.140	0.084	0.382
26	0.170	0.587	0.520	0.788	5.10	17.0	3.30	0.788	0.721	0.140	0.084	0.382
27	0.170	0.587	0.520	0.788	6.00	16.2	3.30	0.788	0.721	0.140	0.084	0.290
28	0.170	0.520	0.520	0.788	5.82	15.4	3.30	0.721	0.721	0.140	0.084	0.290
29	0.170	0.520	0.520	0.788	-----	14.3	3.30	0.721	0.788	0.140	0.084	0.290
30	0.170	0.520	0.520	0.788	-----	13.6	3.15	0.721	1.13	0.121	0.084	0.290
31	0.170	-----	0.520	0.788	-----	13.6	-----	0.587	-----	0.121	0.084	-----
Maks.	0.200	3.00	0.788	1.13	7.25	19.0	17.4	3.90	1.73	1.54	0.230	3.15
Min.	0.102	0.170	0.382	0.520	0.520	3.30	3.15	0.587	0.428	0.121	0.046	0.084
Ortalama	0.140	0.424	0.498	0.628	2.79	7.67	6.04	2.06	0.674	0.598	0.095	0.216
LT/SN/Km2	0.895	2.71	3.18	4.02	17.8	49.0	38.6	13.2	4.31	3.82	0.605	1.38
AKIM mm.	2.40	7.03	8.52	10.8	43.1	131.	100.	35.2	11.2	10.2	1.62	3.57
MİL. M3	0.375	1.10	1.33	1.68	6.74	20.5	15.6	5.51	1.75	1.60	0.253	0.559

SU YILI (2006) YILLIK TOPLAM AKIM 57.00 MİLYON M3 364 MM. 11.6 LT/SN/Km2

14. Yesilırmak Havzasi

D14A137 ACIPINAR DERE DOĞANŞAR

YERİ : **SİVAS -DOĞANŞAR İLÇESİ GÜNEY-BATISINDADIR.**
37°30'26" Doğu - 40°11'12" Kuzey

YAĞIŞ ALANI : **35,00 km2** **YAKLAŞIK KOT : 1350 m**

GÖZLEM SÜRESİ : **01.10.1996 – 30.09.2006**

ORTALAMA AKIMLAR : **Gözlem süresinde 0.534 m3/sn. (10 Yıllık) 2006 Su yılında 0.594 m3/sn.**

ANLIK EN ÇOK VE EN AZ AKIMLAR:

2006 Su yılında anlık ençok akım	:	**4.02**	**m3/sn**	**07.05.2006**
2006 Su yılında anlık enaz akım	:	**0.110**	**m3/sn**	**01.08.2006**
Gözlem süresinde anlık ençok akım	:	**6.42**	**m3/sn**	**20.04.2000**
Gözlem süresinde anlık enaz akım	:	**0.055**	**m3/sn**	**27.10.2003**

Akımlar 01 Ekim 2005 'den 30 Eylül 2006' a kadar m3/sn olarak

Gün	Ekim	Kasım	Aralık	Ocak	Şubat	Mart	Nisan	Mayıs	Haziran	Temmuz	Ağustos	Eylül
01	0.165	0.230	0.230	0.325	0.230	0.420	1.39	1.95	0.920	0.240	0.150	0.290
02	0.165	0.230	0.230	0.325	0.230	0.420	1.95	1.95	0.820	0.240	0.150	0.290
03	0.165	0.230	0.230	0.325	0.230	0.510	1.95	1.81	0.710	0.240	0.150	0.290
04	0.165	0.230	0.230	0.230	0.230	0.696	1.67	1.81	0.710	0.240	0.110	0.290
05	0.165	0.230	0.230	0.230	0.230	0.696	1.53	1.95	0.600	0.240	0.110	0.290
06	0.165	0.230	0.230	0.230	0.230	0.696	1.25	2.40	0.600	0.240	0.110	0.290
07	0.165	0.230	0.230	0.230	0.230	0.696	1.14	3.53	0.600	0.240	0.110	0.290
08	0.165	0.230	0.230	0.230	0.230	0.888	1.39	3.20	0.510	0.240	0.110	0.290
09	0.165	0.230	0.230	0.230	0.325	1.08	2.25	2.55	0.420	0.240	0.110	0.290
10	0.165	0.230	0.230	0.230	0.325	1.08	2.55	2.25	0.420	0.240	0.110	0.290
11	0.165	0.230	0.230	0.230	0.325	1.08	2.40	2.10	0.420	0.190	0.110	0.290
12	0.165	0.230	0.230	0.230	0.325	0.984	2.40	2.10	0.420	0.190	0.110	0.290
13	0.165	0.230	0.230	0.230	0.325	0.888	2.70	2.10	0.420	0.190	0.110	0.290
14	0.165	0.230	0.230	0.230	0.325	0.888	2.87	1.81	0.420	0.190	0.110	0.290
15	0.165	0.230	0.230	0.230	0.325	0.888	3.20	1.67	0.420	0.190	0.110	0.290
16	0.165	0.230	0.230	0.230	0.325	0.888	3.03	1.81	0.420	0.190	0.190	0.290
17	0.230	0.230	0.230	0.230	0.325	0.888	2.40	1.95	0.355	0.150	0.355	0.290
18	0.230	0.230	0.230	0.230	0.325	0.888	2.10	1.67	0.355	0.150	0.290	0.290
19	0.230	0.230	0.325	0.230	0.325	0.888	1.95	1.67	0.355	0.150	0.290	0.290
20	0.230	0.230	0.325	0.230	0.325	0.888	2.10	1.67	0.355	0.150	0.290	0.240
21	0.230	0.230	0.325	0.230	0.325	0.792	2.10	1.67	0.355	0.150	0.290	0.290
22	0.230	0.230	0.325	0.230	0.325	0.792	1.95	1.67	0.290	0.150	0.290	0.240
23	0.230	0.230	0.325	0.230	0.325	0.792	1.95	1.53	0.355	0.150	0.290	0.240
24	0.230	0.230	0.325	0.230	0.325	0.888	1.67	1.53	0.290	0.150	0.290	0.240
25	0.230	0.230	0.325	0.230	0.325	1.65	1.53	1.53	0.290	0.150	0.290	0.240
26	0.230	0.230	0.325	0.230	0.325	1.53	1.53	1.67	0.290	0.150	0.290	0.240
27	0.230	0.230	0.325	0.230	0.420	1.14	1.53	1.67	0.240	0.150	0.290	0.240
28	0.230	0.230	0.325	0.230	0.420	1.02	1.53	1.53	0.240	0.150	0.290	0.240
29	0.230	0.230	0.325	0.230	-----	1.02	1.53	1.53	0.240	0.150	0.290	0.240
30	0.230	0.230	0.325	0.230	-----	0.920	1.67	1.39	0.240	0.150	0.290	0.190
31	0.230	-----	0.325	0.230	-----	1.02	-----	1.25	-----	0.150	0.290	-----
Maks.	0.230	0.230	0.325	0.325	0.420	2.17	3.69	4.02	0.920	0.240	0.355	0.290
Min.	0.165	0.230	0.230	0.230	0.230	0.420	1.14	0.920	0.240	0.150	0.110	0.190
Ortalama	0.196	0.230	0.270	0.239	0.305	0.900	1.97	1.90	0.436	0.187	0.206	0.272
LT/SN/Km2	5.61	6.57	7.71	6.83	8.70	25.7	56.4	54.3	12.5	5.34	5.88	7.76
AKIM mm.	15.0	17.0	20.6	18.3	21.1	68.9	146.	145.	32.3	14.3	15.7	20.1
MİL. M3	0.526	0.596	0.723	0.641	0.737	2.41	5.12	5.09	1.13	0.500	0.551	0.704

SU YILI (2006) YILLIK TOPLAM AKIM 18.73 MİLYON M3 535 MM. 17.0 LT/SN/Km2

14. Yesilırmak Havzasi

D14A140 ÇİVRİL D. AĞLAMIŞ

YERİ : **TOKAT-TURHAL İLÇE MERKEZİNDEN AYRILAN ÇİVRİL YOLUNUN 12. KM AĞLAMIŞ MAHALLESİNDEDİR**
25 LİK PAFTADAKİ YERİ: H35-B2
35°57'35" Doğu - 40°23'0" Kuzey

YAĞIŞ ALANI : **78,00 km2** **YAKLAŞIK KOT : 750 m**

GÖZLEM SÜRESİ : **01.09.1997 - 30.09.2006**

ORTALAMA AKIMLAR : **Gözlem süresinde 0.369 m3/sn. (7 Yıllık) 2006 Su yılında 0.197 m3/sn.**

ANLIK EN ÇOK VE EN AZ AKIMLAR:

2006 Su yılında anlık ençok akım	**:**	**4.64**	**m3/sn**	**28.05.2006**
2006 Su yılında anlık enaz akım	**:**	**0.010**	**m3/sn**	**26.06.2006**
Gözlem süresinde anlık ençok akım	**:**	**6.28**	**m3/sn**	**17.08.2002**
Gözlem süresinde anlık enaz akım	**:**	**0.000**	**m3/sn**	**17.06.2001**

İstasyon için kullanılmış anahtar bulunamadı.

Akımlar 01 Ekim 2005 'den 30 Eylül 2006' a kadar m3/sn olarak

Gün	Ekim	Kasım	Aralık	Ocak	Şubat	Mart	Nisan	Mayıs	Haziran	Temmuz	Ağustos	Eylül
01	0.096	0.096	0.120	0.120	0.096	0.420	0.530	0.320	0.420	0.056	0.056	0.039
02	0.096	0.096	0.120	0.120	0.096	0.420	0.530	0.370	0.420	0.056	0.056	0.039
03	0.120	0.096	0.120	0.120	0.120	0.420	0.530	0.420	0.420	0.056	0.056	0.039
04	0.120	0.096	0.120	0.120	0.120	0.420	0.530	0.320	0.420	0.056	0.056	0.039
05	0.096	0.096	0.096	0.120	0.120	0.370	0.530	0.270	0.320	0.056	0.056	0.039
06	0.096	0.096	0.096	0.120	0.120	0.370	0.530	0.270	0.320	0.074	0.056	0.039
07	0.096	0.096	0.096	0.120	0.120	0.370	0.530	0.270	0.320	0.056	0.056	0.039
08	0.096	0.096	0.096	0.120	0.120	0.370	0.530	0.370	0.320	0.056	0.074	0.039
09	0.096	0.096	0.096	0.120	0.120	0.370	0.530	0.370	0.270	0.056	0.074	0.039
10	0.096	0.096	0.096	0.120	0.120	0.370	0.530	0.320	0.270	0.056	0.074	0.039
11	0.096	0.096	0.096	0.120	0.120	0.370	0.530	0.320	0.270	0.056	0.056	0.039
12	0.096	0.096	0.096	0.120	0.150	0.370	0.530	0.320	0.420	0.056	0.056	0.039
13	0.074	0.096	0.096	0.120	0.150	0.370	0.530	0.320	0.420	0.056	0.074	0.039
14	0.056	0.096	0.120	0.120	0.150	0.370	0.530	0.320	0.853	0.228	0.056	0.039
15	0.056	0.096	0.120	0.120	0.150	0.370	0.530	0.270	1.40	0.186	0.056	0.039
16	0.074	0.096	0.120	0.120	0.150	0.370	0.475	0.228	0.096	0.150	0.074	0.039
17	0.096	0.096	0.120	0.120	0.120	0.370	0.475	0.320	0.056	0.120	0.074	0.039
18	0.096	0.096	0.120	0.120	0.150	0.370	0.475	0.320	0.039	0.120	0.056	0.039
19	0.096	0.096	0.120	0.120	0.150	0.370	0.420	0.270	0.056	0.150	0.039	0.039
20	0.096	0.096	0.120	0.120	0.150	0.370	0.420	0.228	0.056	0.120	0.056	0.056
21	0.096	0.120	0.120	0.120	0.186	0.420	0.420	0.228	0.056	0.120	0.056	0.096
22	0.096	0.150	0.120	0.120	0.228	0.593	0.420	0.186	0.056	0.120	0.056	0.150
23	0.096	0.186	0.120	0.120	0.228	0.530	0.420	0.186	0.056	0.120	0.056	0.186
24	0.096	0.150	0.120	0.120	0.228	0.475	0.420	0.186	0.039	0.120	0.056	0.186
25	0.120	0.120	0.120	0.120	0.228	0.475	0.420	0.228	0.039	0.120	0.056	0.186
26	0.120	0.120	0.096	0.096	0.320	0.530	0.420	0.186	0.039	0.120	0.056	0.150
27	0.096	0.120	0.120	0.120	0.420	0.593	0.420	0.270	0.056	0.120	0.056	0.150
28	0.096	0.120	0.120	0.150	0.420	0.530	0.420	0.593	0.056	0.096	0.056	0.120
29	0.096	0.120	0.120	0.120	-----	0.530	0.370	1.50	0.056	0.120	0.039	0.096
30	0.096	0.120	0.120	0.096	-----	0.530	0.320	1.40	0.056	0.074	0.039	0.074
31	0.096	-----	0.120	0.096	-----	0.530	-----	0.420	-----	0.074	0.039	-----
Maks.	0.120	0.186	0.120	0.150	0.475	0.657	0.530	4.64	1.86	0.228	0.096	0.228
Min.	0.056	0.096	0.074	0.074	0.096	0.370	0.320	0.186	0.010	0.018	0.018	0.039
Ortalama	0.095	0.108	0.112	0.119	0.173	0.430	0.476	0.374	0.256	0.098	0.057	0.073
LT/SN/Km2	1.22	1.39	1.44	1.52	2.22	5.52	6.10	4.80	3.28	1.25	0.734	0.936
AKIM mm.	3.27	3.60	3.85	4.07	5.37	14.8	15.8	12.8	8.50	3.35	1.97	2.43
MİL. M3	0.255	0.280	0.301	0.318	0.419	1.15	1.23	1.00	0.663	0.261	0.153	0.189

SU YILI (2006) YILLIK TOPLAM AKIM 6.22 MİLYON M3 80 MM. 2.5 LT/SN/Km2

14. Yesilırmak Havzasi

D14A145 AVCI D. İVERÖNÜ

YERİ : ERBAA-GÖKDERE-TOKAT KARAYOLUNUN 8. KM SOLA AYRILAN YOLUN 3 KM SİNDEKİ İVERÖNÜ KÖYÜNDEDİR
25 LİK PAFTADAKİ YERİ: G37-D4
36°35'36" Doğu - 40°36'44" Kuzey

YAĞIŞ ALANI : 17,50 km2 **YAKLAŞIK KOT** : 430 m

GÖZLEM SÜRESİ : 24.10.1997 - 30.09.2006

ORTALAMA AKIMLAR : Gözlem süresinde 0.079 m3/sn. (6 Yıllık) 2006 Su yılında 0.068 m3/sn.

ANLIK EN ÇOK VE EN AZ AKIMLAR:

2006 Su yılında anlık ençok akım	:	1.03	m3/sn	01.03.2006
2006 Su yılında anlık enaz akım	:	0.000	m3/sn	01.10.2005
Gözlem süresinde anlık ençok akım	:	3.52	m3/sn	02.03.2005
Gözlem süresinde anlık enaz akım	:	0.000	m3/sn	01.10.1997

3. Anahtar Eğrisi (Seviyeler cm olarak)

Seviye	Akım	Seviye	Akım	Seviye	Akım	Seviye	Akım
10	0.000	20	0.049	46	1.1	120	8.7
12	0.001	23	0.110	56	1.9	130	9.8
14	0.004	29	0.260	70	3.2	140	11.0
16	0.011	33	0.400	90	5.3	150	12.4
18	0.025	40	0.710	110	7.5	190	18.0

Akımlar 01 Ekim 2005 'den 30 Eylül 2006' a kadar m3/sn olarak

Gün	Ekim	Kasım	Aralık	Ocak	Şubat	Mart	Nisan	Mayıs	Haziran	Temmuz	Ağustos	Eylül
01	KURU	KURU	0.004	0.002	0.001	0.890	0.185	0.049	0.049	0.001	KURU	KURU
02	KURU	KURU	0.004	0.002	0.002	0.765	0.480	0.066	0.037	0.001	KURU	KURU
03	KURU	KURU	0.004	0.002	0.002	0.765	0.367	0.135	0.037	0.001	KURU	KURU
04	KURU	KURU	0.004	0.002	0.002	0.664	0.300	0.110	0.017	0.001	KURU	KURU
05	KURU	KURU	0.004	0.002	0.002	0.526	0.235	0.088	0.017	0.001	KURU	KURU
06	KURU	KURU	0.004	0.004	0.002	0.526	0.210	0.066	0.017	0.001	KURU	KURU
07	KURU	KURU	0.002	0.160	0.002	0.480	0.185	0.066	0.017	0.001	KURU	KURU
08	KURU	KURU	0.002	0.135	0.017	0.526	0.135	0.185	0.017	0.001	KURU	KURU
09	KURU	KURU	0.002	0.088	0.049	0.526	0.110	0.160	0.017	0.001	KURU	KURU
10	KURU	KURU	0.002	0.066	0.049	0.480	0.160	0.135	0.017	0.001	KURU	KURU
11	KURU	KURU	0.002	0.066	0.235	0.440	0.185	0.110	0.017	0.001	KURU	KURU
12	KURU	KURU	0.004	0.049	0.333	0.440	0.160	0.088	0.011	0.001	KURU	KURU
13	KURU	KURU	0.007	0.037	0.235	0.367	0.135	0.088	0.011	0.001	KURU	KURU
14	KURU	KURU	0.007	0.037	0.210	0.160	0.135	0.135	0.007	0.001	KURU	KURU
15	KURU	KURU	0.007	0.037	0.185	0.088	0.135	0.110	0.007	0.001	KURU	KURU
16	KURU	KURU	0.004	0.037	0.135	0.088	0.110	0.110	0.007	KURU	KURU	KURU
17	KURU	KURU	0.002	0.037	0.110	0.088	0.110	0.400	0.004	KURU	KURU	KURU
18	KURU	KURU	0.002	0.025	0.110	0.066	0.088	0.440	0.004	KURU	KURU	KURU
19	KURU	KURU	0.002	0.025	0.110	0.066	0.088	0.333	0.004	KURU	KURU	KURU
20	KURU	KURU	0.002	0.025	0.160	0.088	0.088	0.210	0.004	KURU	KURU	KURU
21	KURU	KURU	0.002	0.017	0.185	0.110	0.088	0.185	0.002	KURU	KURU	KURU
22	KURU	KURU	0.002	0.017	0.185	0.210	0.066	0.135	0.001	KURU	KURU	KURU
23	KURU	KURU	0.002	0.017	0.185	0.210	0.066	0.088	0.001	KURU	KURU	KURU
24	KURU	KURU	0.002	0.017	0.185	0.160	0.066	0.088	0.001	KURU	KURU	KURU
25	KURU	0.001	0.002	0.017	0.260	0.160	0.066	0.066	0.001	KURU	KURU	KURU
26	KURU	0.004	0.002	0.017	0.400	0.160	0.066	0.049	0.001	KURU	KURU	KURU
27	KURU	0.011	0.002	0.011	0.820	0.185	0.066	0.110	0.001	KURU	KURU	KURU
28	KURU	0.017	0.002	0.007	0.618	0.260	0.066	0.110	0.001	KURU	KURU	KURU
29	KURU	0.025	0.002	0.007	-----	0.300	0.049	0.088	0.001	KURU	KURU	KURU
30	KURU	0.004	0.002	0.007	-----	0.260	0.049	0.049	0.001	KURU	KURU	KURU
31	KURU	-----	0.002	0.004	-----	0.210	-----	0.049	-----	KURU	KURU	-----
Maks.	KURU	0.135	0.007	0.185	0.890	1.03	0.820	0.765	0.049	0.001	0.001	0.001
Min.	KURU	KURU	0.002	0.002	0.001	0.066	0.049	0.049	0.001	0.001	0.001	0.001
Ortalama	KURU	0.002	0.003	0.031	0.171	0.331	0.142	0.132	0.011	0.000	KURU	KURU
LT/SN/Km2	0.000	0.118	0.171	1.80	9.77	18.9	8.09	7.56	0.627	0.028	0.000	0.000
AKIM mm.	0.000	0.306	0.459	4.82	23.6	50.7	21.0	20.2	1.62	0.074	0.000	0.000
MİL. M3	0.000	0.005	0.008	0.084	0.414	0.887	0.367	0.354	0.028	0.001	0.000	0.000

SU YILI (2006) YILLIK TOPLAM AKIM 2.15 MİLYON M3 123 MM. 3.9 LT/SN/Km2

14. Yesilırmak Havzasi

D14A146 ÇİLKORU D. MUSULLU

YERİ : ERBAA-GÖKDERE-TOKAT KARAYOLUNUN 23. KM MUSULLU KÖYÜ ALT KISMINDADIR. 25 LİK PAFTADAKİ YERİ: G37-D3
36°40'7" Doğu - 40°32'9" Kuzey

YAĞIŞ ALANI : 21,20 km2 **YAKLAŞIK KOT** : 966 m

GÖZLEM SÜRESİ : 26.05.1998 - 30.09.2006

ORTALAMA AKIMLAR : Gözlem süresinde 0.251 m3/sn. (7 Yıllık) 2006 Su yılında 0.210 m3/sn.

ANLIK EN ÇOK VE EN AZ AKIMLAR:

2006 Su yılında anlık ençok akım	:	4.20	m3/sn	02.04.2006
2006 Su yılında anlık enaz akım	:	0.004	m3/sn	24.07.2006
Gözlem süresinde anlık ençok akım	:	11.0	m3/sn	02.03.2005
Gözlem süresinde anlık enaz akım	:	0.000	m3/sn	18.07.2000

6. Anahtar Eğrisi (Seviyeler cm olarak)

Seviye	Akım	Seviye	Akım	Seviye	Akım	Seviye	Akım
28	0.001	38	0.170	56	2.0	110	14.0
30	0.007	40	0.250	64	3.3	130	19.0
32	0.023	44	0.500	80	7.2	150	24.0
34	0.060	48	0.860	90	9.5	170	29.0
36	0.110	52	1.3	100	12.0	200	36.0

Akımlar 01 Ekim 2005 'den 30 Eylül 2006' a kadar m3/sn olarak

Gün	Ekim	Kasım	Aralık	Ocak	Şubat	Mart	Nisan	Mayıs	Haziran	Temmuz	Ağustos	Eylül
01	0.020	0.020	0.250	0.150	0.072	0.640	0.640	0.295	0.210	0.052	0.020	0.009
02	0.020	0.020	0.250	0.150	0.072	0.700	3.33	0.340	0.210	0.052	0.020	0.009
03	0.020	0.020	0.210	0.150	0.072	0.700	1.95	0.510	0.210	0.052	0.020	0.009
04	0.020	0.037	0.210	0.150	0.072	0.700	1.03	0.510	0.210	0.052	0.020	0.009
05	0.020	0.037	0.210	0.150	0.072	0.580	0.700	0.390	0.150	0.052	0.014	0.009
06	0.020	0.037	0.210	0.180	0.072	0.580	0.640	0.390	0.120	0.072	0.014	0.009
07	0.020	0.037	0.210	0.250	0.120	0.580	0.640	0.390	0.120	0.052	0.014	0.009
08	0.020	0.037	0.210	0.250	0.150	0.640	0.640	0.390	0.120	0.052	0.009	0.014
09	0.020	0.037	0.210	0.250	0.210	0.700	0.510	0.390	0.120	0.037	0.009	0.014
10	0.020	0.072	0.210	0.250	0.210	0.580	0.640	0.390	0.120	0.037	0.009	0.014
11	0.020	0.072	0.210	0.250	1.15	0.580	0.510	0.390	0.120	0.030	0.009	0.009
12	0.020	0.072	0.210	0.250	1.03	0.390	0.390	0.340	0.120	0.030	0.009	0.009
13	0.020	0.072	0.210	0.250	0.700	0.390	0.390	0.295	0.093	0.030	0.009	0.009
14	0.020	0.072	0.210	0.250	0.510	0.390	0.390	0.295	0.093	0.030	0.009	0.009
15	0.020	0.072	0.210	0.150	0.390	0.440	0.390	0.295	0.093	0.030	0.009	0.009
16	0.020	0.120	0.210	0.120	0.340	0.390	0.510	0.295	0.072	0.037	0.004	0.009
17	0.020	0.120	0.210	0.120	0.340	0.340	0.390	0.700	0.052	0.037	0.004	0.009
18	0.020	0.120	0.210	0.120	0.295	0.340	0.295	1.03	0.052	0.037	0.004	0.014
19	0.020	0.120	0.210	0.120	0.340	0.340	0.295	0.800	0.052	0.037	0.004	0.014
20	0.020	0.120	0.210	0.120	0.390	0.340	0.295	0.700	0.052	0.037	0.009	0.014
21	0.020	0.120	0.210	0.093	0.440	0.440	0.295	0.700	0.052	0.037	0.009	0.014
22	0.020	0.120	0.210	0.093	0.440	0.510	0.295	0.440	0.052	0.037	0.009	0.020
23	0.020	0.120	0.210	0.093	0.440	0.510	0.295	0.390	0.052	0.037	0.009	0.020
24	0.020	0.180	0.210	0.093	0.440	0.510	0.295	0.295	0.052	0.037	0.014	0.020
25	0.020	0.210	0.210	0.093	0.440	0.510	0.295	0.295	0.052	0.037	0.014	0.020
26	0.020	0.210	0.150	0.093	0.510	0.510	0.295	0.295	0.052	0.037	0.014	0.037
27	0.020	0.250	0.150	0.093	0.700	0.510	0.295	0.340	0.052	0.037	0.014	0.020
28	0.020	0.250	0.150	0.072	0.640	0.510	0.295	0.340	0.052	0.030	0.014	0.020
29	0.020	0.250	0.150	0.072	-----	0.510	0.295	0.295	0.052	0.030	0.014	0.020
30	0.020	0.250	0.150	0.072	-----	0.510	0.295	0.250	0.052	0.030	0.014	0.020
31	0.020	-----	0.150	0.072	-----	0.510	-----	0.210	-----	0.030	0.014	-----
Maks.	0.020	0.250	0.250	0.340	1.95	0.800	4.20	1.03	0.210	0.093	0.037	0.072
Min.	0.020	0.020	0.150	0.052	0.072	0.340	0.295	0.210	0.052	0.004	0.004	0.004
Ortalama	0.020	0.109	0.201	0.149	0.381	0.512	0.584	0.419	0.097	0.039	0.012	0.014
LT/SN/Km2	0.943	5.15	9.48	7.03	18.0	24.2	27.6	19.8	4.57	1.86	0.545	0.662
AKIM mm.	2.53	13.3	25.4	18.8	43.4	64.7	71.4	52.9	11.9	4.99	1.46	1.72
MİL. M3	0.054	0.283	0.538	0.399	0.921	1.37	1.51	1.12	0.251	0.106	0.031	0.036

SU YILI (2006) YILLIK TOPLAM AKIM 6.62 MİLYON M3 312 MM. 9.9 LT/SN/Km2

14. Yesilırmak Havzasi

D14A157 YEŞİLIRMAK N. PAZAR KÖPRÜSÜ

YERİ : TOKAT-PAZAR İLÇESİNDEN OVALI KÖYÜNE GİDEN KARAYOLU ÜZERİNDEKİ DEMİR AYAKLI KÖPRÜDEDİR
25 LİK PAFTADA YERİ: H36-B4
36°16'50" Doğu - 40°17'17" Kuzey

YAĞIŞ ALANI : 3550,00 km2 **YAKLAŞIK KOT** : 545 m

GÖZLEM SÜRESİ : 10.12.2001 - 30.09.2006

ORTALAMA AKIMLAR : Gözlem süresinde 6.962 m3/sn. (3 Yıllık) 2006 Su yılında 6.205 m3/sn.

ANLIK EN ÇOK VE EN AZ AKIMLAR:

2006 Su yılında anlık ençok akım	: 18.6	m3/sn	26.09.2006
2006 Su yılında anlık enaz akım	: 2.95	m3/sn	16.11.2005
Gözlem süresinde anlık ençok akım	: 38.3	m3/sn	06.03.2004
Gözlem süresinde anlık enaz akım	: 1.38	m3/sn	30.01.2003

2. Anahtar Eğrisi (Seviyeler cm olarak)

Seviye	Akım	Seviye	Akım	Seviye	Akım	Seviye	Akım
43	0.100	63	1.8	100	7.7	250	32.0
53	0.170	69	2.8	120	11.4	300	41.0
55	0.430	74	3.6	150	16.0	350	50.0
57	0.780	80	4.6	190	22.0	400	59.0
59	1.1	90	6.2	220	27.0	450	69.0

Akımlar 01 Ekim 2005 'den 30 Eylül 2006' a kadar m3/sn olarak

Gün	Ekim	Kasım	Aralık	Ocak	Şubat	Mart	Nisan	Mayıs	Haziran	Temmuz	Ağustos	Eylül
01	13.4	3.60	3.38	2.95	2.95	5.40	6.20	4.30	6.52	7.70	9.10	9.87
02	12.7	3.60	3.38	2.95	2.95	6.00	8.75	5.03	6.36	7.42	8.90	9.30
03	11.9	3.38	3.17	2.95	2.95	6.20	12.0	6.40	5.40	7.90	8.70	8.70
04	10.2	3.38	3.17	2.95	2.95	7.80	10.3	6.40	5.24	8.70	8.70	9.87
05	9.67	3.38	3.17	2.95	2.95	7.00	8.90	5.60	4.76	8.70	9.87	10.2
06	9.35	3.38	3.17	2.95	2.95	6.00	7.80	5.20	3.80	9.30	8.90	9.87
07	7.80	3.17	3.17	2.95	2.95	5.40	7.16	4.87	3.45	7.70	8.30	10.7
08	7.32	3.17	3.17	2.95	2.95	5.40	6.40	5.60	5.40	8.90	8.70	10.6
09	6.00	3.38	3.17	2.95	3.38	6.80	6.20	5.80	6.52	9.50	8.30	10.4
10	6.40	3.38	3.17	2.95	3.60	6.40	6.20	5.20	9.70	8.70	8.10	11.9
11	5.80	3.38	3.17	2.95	3.77	5.60	6.20	3.93	8.10	8.70	7.14	16.0
12	5.03	3.38	3.17	2.95	7.32	5.03	5.80	3.77	7.42	8.30	8.70	12.0
13	4.70	3.38	3.17	2.95	7.48	4.50	5.40	3.77	6.84	7.70	7.42	12.2
14	4.50	3.17	3.17	2.95	6.20	4.30	5.03	3.93	6.20	8.30	8.50	11.9
15	4.10	3.17	3.17	2.95	5.60	4.30	4.87	3.77	6.52	8.30	8.50	11.9
16	3.93	2.95	3.17	2.95	4.87	4.87	4.87	10.8	6.52	8.70	9.30	12.2
17	3.77	2.95	3.17	2.95	4.30	5.03	4.50	16.0	6.68	8.50	8.90	11.9
18	3.60	2.95	3.17	2.95	4.10	4.70	4.10	16.7	7.14	7.42	8.90	11.6
19	3.60	2.95	3.17	2.95	4.10	4.70	3.77	13.9	7.00	8.50	8.90	11.6
20	3.38	3.17	3.17	2.95	4.70	4.87	3.77	10.7	7.00	8.90	9.70	11.4
21	3.38	3.17	3.17	2.95	4.87	4.70	3.60	7.90	7.00	8.70	9.70	10.2
22	3.38	3.17	3.17	2.95	4.70	4.70	3.77	7.42	6.68	9.10	9.10	13.2
23	3.38	3.38	3.17	2.95	4.30	5.03	3.60	7.28	6.68	9.50	8.90	13.2
24	3.77	3.38	3.17	2.95	4.50	4.87	3.38	6.36	6.20	6.68	9.30	11.6
25	3.60	3.38	3.17	2.95	4.30	6.00	3.60	6.84	7.00	7.90	9.70	13.9
26	3.60	3.17	3.17	2.95	4.50	7.16	3.77	6.68	7.00	8.90	9.87	17.8
27	3.77	3.17	3.17	2.95	5.03	7.16	3.77	8.10	6.68	8.70	10.2	17.1
28	3.77	3.38	3.17	2.95	5.40	7.16	3.77	11.2	7.00	8.50	9.87	18.0
29	3.77	3.38	3.17	2.95	-----	7.00	3.60	9.10	7.28	8.70	9.30	18.0
30	3.77	3.38	3.17	2.95	-----	6.60	4.30	8.30	7.28	9.10	9.70	13.0
31	3.60	-----	2.95	2.95	-----	6.20	-----	8.30	-----	9.10	10.2	-----
Maks.	13.4	3.60	3.38	2.95	7.80	8.60	12.5	17.3	11.4	10.0	12.4	18.6
Min.	3.38	2.95	2.95	2.95	2.95	4.10	3.38	3.77	2.97	5.08	5.40	5.72
Ortalama	5.71	3.27	3.18	2.95	4.31	5.71	5.51	7.39	6.51	8.47	9.01	12.3
LT/SN/Km2	1.61	0.922	0.895	0.831	1.21	1.61	1.55	2.08	1.83	2.39	2.54	3.48
AKIM mm.	4.31	2.39	2.40	2.23	2.94	4.30	4.03	5.58	4.75	6.39	6.80	9.01
MİL. M3	15.3	8.49	8.51	7.90	10.4	15.3	14.3	19.8	16.9	22.7	24.1	32.0

SU YILI (2006) YILLIK TOPLAM AKIM 195.70 MİLYON M3 55 MM. 1.7 LT/SN/Km2

14. Yesilırmak Havzasi

D14A159 FINDICAK D. DALDERE

YERİ : **SAMSUN-LADİK İLÇE MERKEZİNDEN 23 KM MESAFEDEKİ DALDERE KÖYÜNDEKİ BETONARME KÖPRÜDEDİR**
25 LİK PAFTADAKİ YERİ: G36-A1
36°6'7" Doğu - 45°55'14" Kuzey

YAĞIŞ ALANI : **17,10 km2** **YAKLAŞIK KOT : 936 m**

GÖZLEM SÜRESİ : **01.10.2004 - 30.09.2006**

ORTALAMA AKIMLAR : **Gözlem süresinde 0.218 m3/sn. (2 Yıllık) 2006 Su yılında 0.246 m3/sn.**

ANLIK EN ÇOK VE EN AZ AKIMLAR:

2006 Su yılında anlık ençok akım	:	**3.97**	**m3/sn**	**17.05.2006**
2006 Su yılında anlık enaz akım	:	**0.001**	**m3/sn**	**11.08.2006**
Gözlem süresinde anlık ençok akım	:	**32.0**	**m3/sn**	**02.06.2005**
Gözlem süresinde anlık enaz akım	:	**0.001**	**m3/sn**	**11.08.2006**

3. Anahtar Eğrisi (Seviyeler cm olarak)

Seviye	Akım	Seviye	Akım	Seviye	Akım	Seviye	Akım
10	0.000	25	0.150	60	3.8	130	22.0
13	0.001	28	0.270	80	8.0	140	25.0
16	0.007	31	0.440	90	10.4	160	32.0
19	0.026	40	1.1	100	13.3	190	42.0
22	0.068	50	2.4	110	16.0		

Akımlar 01 Ekim 2005 'den 30 Eylül 2006' a kadar m3/sn olarak

Gün	Ekim	Kasım	Aralık	Ocak	Şubat	Mart	Nisan	Mayıs	Haziran	Temmuz	Ağustos	Eylül
01	0.032	0.019	0.110	0.250	0.110	1.00	1.20	0.820	0.032	0.140	0.012	0.012
02	0.019	0.019	0.110	0.180	0.110	0.755	1.48	0.110	0.032	0.110	0.012	0.019
03	0.019	0.019	0.110	0.180	0.110	1.00	1.48	0.076	0.032	0.076	0.007	0.019
04	0.032	0.032	0.110	0.180	0.140	0.625	1.40	0.076	0.032	0.048	0.007	0.019
05	0.032	0.110	0.140	0.250	0.180	0.420	1.40	0.076	0.032	0.032	0.012	0.019
06	0.019	0.076	0.140	0.420	0.310	0.420	1.20	0.076	0.032	0.032	0.012	0.019
07	0.012	0.048	0.140	0.490	0.690	0.420	1.10	0.076	0.032	0.032	0.012	0.019
08	0.012	0.048	0.140	0.420	0.490	0.420	1.10	0.076	0.048	0.032	0.012	0.019
09	0.012	0.048	0.110	0.250	0.490	0.365	1.10	0.076	0.048	0.032	0.019	0.019
10	0.012	0.048	0.110	0.180	0.490	0.365	1.30	0.076	0.048	0.032	0.019	0.019
11	0.012	0.048	0.110	0.180	1.57	0.250	1.30	0.076	0.048	0.019	0.019	0.019
12	0.012	0.048	0.076	0.140	0.820	0.250	1.10	0.076	0.048	0.019	0.019	0.019
13	0.012	0.048	0.076	0.140	0.490	0.250	1.10	0.110	0.076	0.019	0.019	0.019
14	0.012	0.048	0.048	0.140	0.420	0.250	1.10	0.180	0.076	0.019	0.019	0.019
15	0.019	0.048	0.048	0.140	0.365	0.250	1.10	0.140	0.076	0.019	0.019	0.012
16	0.019	0.048	0.048	0.110	0.365	0.250	1.10	0.180	0.076	0.019	0.019	0.012
17	0.032	0.076	0.048	0.110	0.365	0.250	1.10	1.40	0.076	0.019	0.012	0.012
18	0.032	0.076	0.048	0.110	0.110	0.250	1.10	1.00	0.076	0.019	0.012	0.012
19	0.048	0.110	0.048	0.110	0.180	0.250	1.10	0.365	0.076	0.019	0.012	0.012
20	0.032	0.110	0.048	0.110	0.420	0.490	0.910	0.140	0.048	0.019	0.012	0.012
21	0.019	0.140	0.048	0.110	0.420	0.755	0.910	0.048	0.048	0.019	0.012	0.012
22	0.019	0.250	0.048	0.110	0.420	1.20	0.910	0.048	0.048	0.019	0.012	0.048
23	0.019	0.250	0.076	0.110	0.490	0.755	0.910	0.032	0.076	0.012	0.012	0.110
24	0.019	0.250	0.076	0.076	0.690	0.755	1.00	0.032	0.076	0.012	0.012	0.048
25	0.019	0.365	0.076	0.076	1.20	0.690	1.10	0.032	0.076	0.012	0.012	0.048
26	0.019	0.310	0.076	0.076	1.20	0.690	1.10	0.032	0.076	0.012	0.012	0.032
27	0.019	0.180	0.076	0.076	1.20	0.755	0.910	0.310	0.076	0.019	0.012	0.032
28	0.019	0.140	0.076	0.076	0.755	1.73	0.910	0.140	0.076	0.012	0.007	0.019
29	0.019	0.110	0.076	0.110	-----	1.57	0.910	0.048	0.250	0.012	0.007	0.019
30	0.019	0.110	0.110	0.110	-----	1.40	0.820	0.032	0.250	0.012	0.007	0.019
31	0.019	-----	0.140	0.110	-----	1.40	-----	0.032	-----	0.012	0.007	-----
Maks.	0.076	0.625	0.310	0.690	2.83	1.90	2.28	3.97	2.40	0.180	0.048	0.180
Min.	0.012	0.019	0.048	0.048	0.007	0.250	0.820	0.032	0.032	0.012	0.001	0.012
Ortalama	0.021	0.108	0.087	0.165	0.521	0.653	1.11	0.193	0.070	0.029	0.013	0.024
LT/SN/Km2	1.21	6.30	5.09	9.68	30.5	38.2	64.8	11.3	4.09	1.71	0.751	1.40
AKIM mm.	3.23	16.3	13.6	25.9	73.8	102.	168.	30.3	10.6	4.59	2.01	3.63
MİL. M3	0.055	0.279	0.233	0.443	1.26	1.75	2.87	0.518	0.181	0.079	0.034	0.062

SU YILI (2006) YILLIK TOPLAM AKIM 7.76 MİLYON M3 454 MM. 14.4 LT/SN/Km2

14. Yesilırmak Havzasi

D14A161 İSHAK DERE CİZÖZÜ

YERİ : **SİVAS-YILDIZELİ İlçesi Cizözü Köyü çıkışındaki deredeydir.**
36°23'41" Doğu - 39°57'16" Kuzey

YAĞIŞ ALANI : **13,00 km2** **YAKLAŞIK KOT : 1332 m**

GÖZLEM SÜRESİ : **01.10.2004 - 30.09.2006**

ORTALAMA AKIMLAR : **Gözlem süresinde 0.051 m3/sn. (2 Yıllık) 2006 Su yılında 0.039 m3/sn.**

ANLIK EN ÇOK VE EN AZ AKIMLAR:

2006 Su yılında anlık ençok akım	**:**	**1.21**	**m3/sn**	**16.05.2006**
2006 Su yılında anlık enaz akım	**:**	**0.000**	**m3/sn**	**01.10.2005**
Gözlem süresinde anlık ençok akım	**:**	**1.43**	**m3/sn**	**02.03.2005**
Gözlem süresinde anlık enaz akım	**:**	**0.000**	**m3/sn**	**01.10.2004**

Akımlar 01 Ekim 2005 'den 30 Eylül 2006' a kadar m3/sn olarak

Gün	Ekim	Kasım	Aralık	Ocak	Şubat	Mart	Nisan	Mayıs	Haziran	Temmuz	Ağustos	Eylül
01	KURU	0.007	0.018	0.011	0.027	0.027	0.179	0.149	0.057	KURU	KURU	KURU
02	KURU	0.007	0.011	0.011	0.027	0.027	0.324	0.210	0.057	KURU	KURU	KURU
03	KURU	0.007	0.011	0.011	0.027	0.027	0.324	0.210	0.042	KURU	KURU	KURU
04	KURU	0.007	0.011	0.011	0.027	0.027	0.210	0.149	0.018	KURU	KURU	KURU
05	KURU	0.018	0.011	0.011	0.027	0.027	0.210	0.149	0.018	KURU	KURU	KURU
06	KURU	0.011	0.011	0.011	0.027	0.042	0.179	0.149	0.018	KURU	KURU	KURU
07	KURU	0.011	0.011	0.011	0.027	0.042	0.179	0.118	0.027	KURU	KURU	KURU
08	KURU	0.011	0.011	0.011	0.027	0.027	0.179	0.149	0.027	KURU	KURU	KURU
09	KURU	0.011	0.011	0.011	0.027	0.042	0.149	0.149	0.027	KURU	KURU	KURU
10	0.005	0.011	0.011	0.011	0.027	0.057	0.149	0.149	0.027	KURU	KURU	KURU
11	0.005	0.011	0.011	0.011	0.027	0.057	0.149	0.118	0.018	KURU	KURU	KURU
12	0.005	0.011	0.011	0.018	0.027	0.057	0.118	0.088	0.011	KURU	KURU	KURU
13	0.005	0.011	0.011	0.018	0.027	0.088	0.088	0.088	0.011	KURU	KURU	KURU
14	0.005	0.011	0.011	0.018	0.027	0.118	0.088	0.088	0.011	KURU	KURU	KURU
15	0.003	0.011	0.011	0.018	0.027	0.118	0.149	0.088	0.018	KURU	KURU	KURU
16	0.005	0.011	0.018	0.018	0.027	0.088	0.179	0.149	0.011	KURU	KURU	KURU
17	0.007	0.011	0.018	0.018	0.027	0.088	0.149	0.267	0.011	KURU	KURU	KURU
18	0.005	0.011	0.018	0.027	0.027	0.088	0.118	0.179	0.011	KURU	KURU	KURU
19	0.007	0.011	0.018	0.027	0.027	0.088	0.088	0.149	0.007	KURU	KURU	KURU
20	0.007	0.011	0.018	0.027	0.027	0.088	0.088	0.149	0.005	KURU	KURU	KURU
21	0.007	0.018	0.018	0.027	0.027	0.118	0.088	0.149	KURU	KURU	KURU	KURU
22	0.007	0.027	0.018	0.027	0.027	0.149	0.057	0.118	KURU	KURU	KURU	KURU
23	0.007	0.027	0.018	0.027	0.027	0.149	0.057	0.088	KURU	KURU	KURU	KURU
24	0.007	0.018	0.018	0.027	0.027	0.179	0.057	0.088	KURU	KURU	KURU	KURU
25	0.005	0.018	0.011	0.027	0.027	0.324	0.088	0.057	KURU	KURU	KURU	KURU
26	0.005	0.018	0.011	0.027	0.027	0.324	0.088	0.088	KURU	KURU	KURU	KURU
27	0.005	0.018	0.011	0.027	0.027	0.210	0.088	0.149	KURU	KURU	KURU	KURU
28	0.005	0.018	0.011	0.027	0.027	0.179	0.088	0.118	KURU	KURU	KURU	KURU
29	0.007	0.018	0.011	0.027	-----	0.149	0.088	0.088	KURU	KURU	KURU	0.007
30	0.007	0.018	0.011	0.027	-----	0.149	0.118	0.088	KURU	KURU	KURU	0.007
31	0.007	-----	0.011	0.027	-----	0.149	-----	0.057	-----	KURU	KURU	-----
Maks.	0.007	0.088	0.042	0.027	0.027	0.702	0.840	1.21	0.057	KURU	KURU	0.088
Min.	KURU	0.007	0.011	0.011	0.027	0.027	0.057	0.057	KURU	KURU	KURU	KURU
Ortalama	0.004	0.014	0.013	0.020	0.027	0.107	0.137	0.130	0.014	KURU	KURU	0.000
LT/SN/Km2	0.318	1.05	1.02	1.51	2.08	8.19	10.5	10.0	1.11	0.000	0.000	0.036
AKIM mm.	0.851	2.72	2.73	4.03	5.02	21.9	27.3	26.8	2.87	0.000	0.000	0.093
MİL. M3	0.011	0.035	0.036	0.052	0.065	0.285	0.355	0.348	0.037	0.000	0.000	0.001

SU YILI (2006) YILLIK TOPLAM AKIM 1.22 MİLYON M3 94 MM. 3.0 LT/SN/Km2

14. Yesilırmak Havzasi

D14A162 YEŞİLIRMAK KOZLU

YERİ : **SİVAS DOĞANŞAR İlçesi Kozlu Köyündeki Köprüdedir.**
37°33'4" Doğu - 40°15'14" Kuzey

YAĞIŞ ALANI : **712,62 km2** **YAKLAŞIK KOT : 1027 m**

GÖZLEM SÜRESİ : **01.10.2004 - 30.09.2006**

ORTALAMA AKIMLAR : **Gözlem süresinde 11.132 m3/sn. (2 Yıllık) 2006 Su yılında 13.120 m3/sn.**

ANLIK EN ÇOK VE EN AZ AKIMLAR:

2006 Su yılında anlık ençok akım	:	**132.**	**m3/sn**	**25.03.2006**
2006 Su yılında anlık enaz akım	:	**0.840**	**m3/sn**	**22.08.2006**
Gözlem süresinde anlık ençok akım	:	**132.**	**m3/sn**	**25.03.2006**
Gözlem süresinde anlık enaz akım	:	**0.585**	**m3/sn**	**01.10.2004**

Akımlar 01 Ekim 2005 'den 30 Eylül 2006' a kadar m3/sn olarak

Gün	Ekim	Kasım	Aralık	Ocak	Şubat	Mart	Nisan	Mayıs	Haziran	Temmuz	Ağustos	Eylül
01	1.66	2.56	2.74	2.92	2.38	12.2	50.0	42.8	19.5	5.03	1.95	1.65
02	1.48	2.56	2.74	2.92	2.38	14.5	54.8	49.8	18.5	5.03	1.95	1.49
03	1.48	2.74	2.56	2.92	2.20	18.1	51.6	49.1	18.0	5.03	1.80	1.65
04	1.84	2.74	2.56	2.92	2.20	23.5	51.6	41.4	17.0	4.72	1.65	1.80
05	1.84	3.42	2.56	2.92	2.20	17.5	42.0	46.3	16.0	4.72	1.65	1.95
06	1.66	3.42	2.38	3.10	2.56	20.2	32.0	51.9	15.0	5.03	1.49	1.95
07	1.66	3.42	2.38	3.42	5.02	27.7	31.3	82.0	14.5	5.03	1.32	1.95
08	1.66	3.42	2.20	3.42	6.30	49.2	40.4	76.4	14.0	4.72	1.32	2.17
09	1.48	3.10	2.20	3.10	6.77	57.2	57.2	58.8	13.0	4.10	1.49	2.17
10	1.48	2.74	2.20	2.92	5.34	41.2	68.4	49.1	12.0	3.89	1.49	2.17
11	1.48	2.56	2.20	2.74	5.66	20.8	63.6	44.2	11.5	3.67	1.32	2.17
12	1.48	2.56	2.20	2.74	9.12	17.5	55.6	40.7	11.0	3.67	1.32	2.38
13	1.30	2.38	2.02	2.74	10.1	18.8	58.0	40.7	10.6	3.46	1.32	2.38
14	1.30	2.38	2.02	2.74	8.18	23.5	54.8	37.9	10.6	3.03	1.32	2.38
15	1.30	2.20	2.02	2.56	6.77	42.8	56.4	34.4	11.0	2.81	1.32	2.38
16	1.66	2.20	2.92	2.38	6.30	29.1	52.6	33.0	9.48	2.81	1.32	2.38
17	5.02	2.20	2.74	2.38	5.66	27.7	45.6	38.6	8.72	2.81	1.32	2.38
18	2.92	2.20	2.56	2.38	5.34	27.7	38.6	33.7	8.34	2.81	1.49	2.38
19	5.66	2.02	3.74	2.38	5.34	27.7	35.1	31.8	7.58	2.60	1.49	2.17
20	4.06	2.02	6.30	2.38	5.34	27.7	35.8	30.0	7.20	2.81	1.49	2.17
21	3.10	2.56	5.02	2.20	5.34	27.7	35.8	28.8	6.89	2.60	1.32	2.60
22	2.56	3.42	4.38	2.56	5.34	27.7	33.7	27.6	6.58	2.60	1.32	2.81
23	2.38	2.92	4.38	2.38	5.66	27.7	33.0	27.0	6.27	2.60	1.32	2.81
24	2.20	2.92	4.06	2.38	5.98	32.8	39.3	26.4	5.96	2.60	1.32	2.81
25	2.02	2.74	3.74	2.38	6.30	99.0	42.1	25.2	5.34	2.60	1.32	2.60
26	2.02	2.74	3.42	2.38	7.71	92.6	35.8	26.4	5.34	2.60	1.19	2.60
27	2.02	2.92	3.42	2.38	9.12	85.4	33.7	31.2	5.34	2.38	1.19	2.38
28	2.02	2.92	3.10	2.20	9.59	85.4	31.8	28.2	5.34	2.38	1.19	2.17
29	2.02	2.92	3.42	2.20	-----	85.4	31.8	24.0	5.34	1.95	1.19	2.17
30	2.02	2.92	2.92	2.38	-----	84.5	51.9	21.0	5.03	1.95	1.32	1.95
31	2.38	-----	2.92	2.20	-----	42.8	-----	20.0	-----	1.95	1.32	-----
Maks.	7.24	3.74	8.18	3.42	11.6	132.	89.0	102.	21.0	5.65	2.17	3.46
Min.	1.30	2.02	2.02	2.02	2.02	11.0	27.0	19.0	5.03	1.80	0.840	1.32
Ortalama	2.17	2.73	3.03	2.63	5.72	39.9	44.8	38.7	10.4	3.35	1.41	2.23
LT/SN/Km2	3.04	3.83	4.26	3.69	8.03	55.9	62.9	54.2	14.5	4.71	1.98	3.13
AKIM mm.	8.14	9.92	11.4	9.90	19.4	150.	163.	145.	37.7	12.6	5.31	8.13
MİL. M3	5.80	7.07	8.12	7.05	13.8	107.	116.	104.	26.9	8.98	3.79	5.79

SU YILI (2006) YILLIK TOPLAM AKIM 414.30 MİLYON M3 581 MM. 18.4 LT/SN/Km2

14. Yesilırmak Havzasi

D14A163 TAHTALI DERE EŞMEBAŞI

YERİ : **SİVAS-YILDIZELI İLÇESI EŞMEBAŞI KÖYÜ ÇIKIŞINDAKI KÖPRÜDEDIR**
36°7'30" Doğu - 39°45'4" Kuzey

YAĞIŞ ALANI : **34,50 km2** **YAKLAŞIK KOT : 1288 m**

GÖZLEM SÜRESİ : **01.10.2005 - 30.09.2006**

ORTALAMA AKIMLAR : **Gözlem süresinde 0.074 m3/sn. (1 Yıllık) 2006 Su yılında 0.074 m3/sn.**

ANLIK EN ÇOK VE EN AZ AKIMLAR:

2006 Su yılında anlık ençok akım	**:**	**0.425 m3/sn**	**02.04.2006**
2006 Su yılında anlık enaz akım	**:**	**0.000 m3/sn**	**18.08.2006**
Gözlem süresinde anlık ençok akım	**:**	**0.425 m3/sn**	**02.04.2006**
Gözlem süresinde anlık enaz akım	**:**	**0.000 m3/sn**	**18.08.2006**

Akımlar 01 Ekim 2005 'den 30 Eylül 2006' a kadar m3/sn olarak

Gün	Ekim	Kasım	Aralık	Ocak	Şubat	Mart	Nisan	Mayıs	Haziran	Temmuz	Ağustos	Eylül
01	0.013	0.025	0.025	0.025	0.052	0.072	0.160	0.235	0.160	0.037	0.007	KURU
02	0.016	0.025	0.025	0.025	0.052	0.072	0.285	0.285	0.142	0.037	0.007	KURU
03	0.016	0.025	0.025	0.025	0.044	0.107	0.355	0.320	0.142	0.037	0.007	KURU
04	0.020	0.030	0.025	0.025	0.052	0.125	0.320	0.320	0.125	0.030	0.007	KURU
05	0.020	0.061	0.025	0.025	0.044	0.107	0.320	0.285	0.125	0.030	0.007	KURU
06	0.020	0.044	0.025	0.025	0.052	0.107	0.285	0.320	0.142	0.044	0.007	KURU
07	0.025	0.037	0.025	0.030	0.044	0.107	0.260	0.285	0.125	0.052	0.007	KURU
08	0.025	0.030	0.025	0.025	0.044	0.142	0.260	0.320	0.107	0.044	0.007	KURU
09	0.025	0.030	0.025	0.025	0.044	0.142	0.260	0.285	0.107	0.037	0.007	KURU
10	0.025	0.030	0.025	0.025	0.044	0.142	0.235	0.285	0.090	0.037	0.007	KURU
11	0.025	0.030	0.025	0.025	0.052	0.125	0.235	0.285	0.090	0.030	0.007	KURU
12	0.025	0.025	0.025	0.025	0.052	0.142	0.235	0.285	0.107	0.030	0.007	KURU
13	0.025	0.025	0.025	0.025	0.044	0.090	0.235	0.285	0.090	0.030	0.007	KURU
14	0.025	0.025	0.025	0.025	0.044	0.072	0.210	0.260	0.090	0.030	0.007	KURU
15	0.025	0.025	0.025	0.025	0.044	0.090	0.235	0.260	0.090	0.030	0.007	KURU
16	0.025	0.025	0.025	0.044	0.052	0.090	0.235	0.260	0.090	0.037	0.007	KURU
17	0.025	0.025	0.025	0.052	0.061	0.090	0.210	0.285	0.072	0.030	0.007	KURU
18	0.025	0.025	0.025	0.061	0.052	0.090	0.210	0.285	0.052	0.030	KURU	KURU
19	0.025	0.025	0.025	0.072	0.052	0.090	0.160	0.260	0.044	0.030	KURU	KURU
20	0.025	0.025	0.025	0.061	0.052	0.090	0.142	0.235	0.044	0.030	KURU	KURU
21	0.025	0.030	0.025	0.061	0.052	0.107	0.142	0.235	0.037	0.030	KURU	KURU
22	0.025	0.030	0.025	0.061	0.052	0.125	0.125	0.210	0.030	0.030	KURU	KURU
23	0.025	0.037	0.025	0.061	0.061	0.125	0.142	0.235	0.030	0.030	KURU	KURU
24	0.025	0.025	0.025	0.061	0.061	0.142	0.185	0.210	0.030	0.030	KURU	KURU
25	0.025	0.025	0.025	0.052	0.061	0.210	0.235	0.185	0.030	0.030	KURU	KURU
26	0.025	0.025	0.030	0.044	0.061	0.260	0.235	0.185	0.030	0.016	KURU	KURU
27	0.025	0.030	0.037	0.052	0.061	0.235	0.235	0.210	0.030	0.007	KURU	KURU
28	0.025	0.030	0.037	0.052	0.061	0.160	0.235	0.185	0.037	0.007	KURU	KURU
29	0.025	0.030	0.030	0.052	-----	0.142	0.235	0.185	0.037	0.007	KURU	KURU
30	0.025	0.025	0.025	0.052	-----	0.142	0.260	0.185	0.037	0.007	KURU	KURU
31	0.025	-----	0.025	0.052	-----	0.142	-----	0.160	-----	0.007	KURU	-----
Maks.	0.030	0.090	0.044	0.090	0.090	0.260	0.425	0.425	0.160	0.061	0.007	KURU
Min.	0.013	0.025	0.025	0.025	0.044	0.061	0.125	0.142	0.030	0.007	KURU	KURU
Ortalama	0.024	0.029	0.026	0.041	0.052	0.125	0.229	0.252	0.079	0.029	0.004	KURU
LT/SN/Km2	0.683	0.849	0.756	1.19	1.50	3.63	6.64	7.32	2.28	0.835	0.111	0.000
AKIM mm.	1.83	2.20	2.03	3.18	3.62	9.72	17.2	19.6	5.92	2.24	0.298	0.000
MİL. M3	0.063	0.076	0.070	0.110	0.125	0.335	0.594	0.676	0.204	0.077	0.010	0.000

SU YILI (2006) YILLIK TOPLAM AKIM 2.34 MİLYON M3 68 MM. 2.2 LT/SN/Km2

14. Yesilırmak Havzasi

D14A164 ÇOBANLI DERE GÜNALAN

YERİ : **SİVAS GÖLOVA İLÇESI GÜNALAN KÖYÜ ÇIKIŞINDAKI KÖPRÜDEDİR**
38°37'34" Doğu - 40°2'6" Kuzey

YAĞIŞ ALANI : **792,00 km2** **YAKLAŞIK KOT : 1245 m**

GÖZLEM SÜRESİ : **01.10.2005 - 30.09.2006**

ORTALAMA AKIMLAR : **Gözlem süresinde 9.606 m3/sn. (1 Yıllık) 2006 Su yılında 9.606 m3/sn.**

ANLIK EN ÇOK VE EN AZ AKIMLAR:

2006 Su yılında anlık ençok akım	:	**97.9**	**m3/sn**	**30.04.2006**
2006 Su yılında anlık enaz akım	:	**0.364**	**m3/sn**	**24.12.2005**
Gözlem süresinde anlık ençok akım	:	**97.9**	**m3/sn**	**30.04.2006**
Gözlem süresinde anlık enaz akım	:	**0.364**	**m3/sn**	**24.12.2005**

Akımlar 01 Ekim 2005 'den 30 Eylül 2006' a kadar m3/sn olarak

Gün	Ekim	Kasım	Aralık	Ocak	Şubat	Mart	Nisan	Mayıs	Haziran	Temmuz	Ağustos	Eylül
01	0.480	0.480	0.480	0.397	1.80	3.30	36.2	56.6	20.0	6.00	2.46	1.90
02	0.480	0.480	0.480	1.70	2.18	3.02	41.0	60.3	19.0	5.70	2.46	2.04
03	0.480	0.480	0.480	1.80	1.90	3.51	33.2	57.5	17.5	5.19	2.32	2.04
04	0.480	0.480	0.480	2.04	1.60	4.35	26.6	52.0	16.0	5.19	2.32	2.04
05	0.480	0.480	0.480	2.18	1.90	3.51	23.8	48.6	14.8	5.40	2.32	2.04
06	0.480	0.480	0.430	2.04	2.04	3.72	19.5	54.8	15.6	6.00	2.18	2.04
07	0.530	0.480	0.430	2.04	2.18	4.98	20.0	54.8	14.4	6.30	1.90	2.04
08	0.480	0.480	0.430	2.04	2.18	9.84	27.3	72.3	13.2	6.30	1.70	2.04
09	0.480	0.480	0.430	2.04	2.18	18.5	47.7	64.2	13.2	5.40	1.80	2.18
10	0.480	0.480	0.430	1.80	2.32	10.9	54.8	52.9	11.6	4.98	1.80	2.46
11	0.480	0.480	0.430	1.80	2.32	6.60	59.4	49.4	10.2	4.56	1.70	2.18
12	0.480	0.480	0.430	1.70	2.46	6.00	55.7	45.1	9.48	4.56	1.80	2.46
13	0.480	0.480	0.430	1.80	2.32	6.00	56.6	46.8	8.10	4.56	1.80	2.18
14	0.480	0.480	0.430	1.70	1.90	7.50	56.6	43.4	7.50	4.14	1.80	2.32
15	0.480	0.480	0.430	1.60	2.18	16.5	57.5	37.0	7.50	3.93	1.90	2.32
16	0.480	0.480	0.430	1.40	1.90	11.3	49.4	35.4	7.50	3.72	1.90	2.32
17	0.480	0.480	0.397	1.40	1.40	9.12	41.8	36.2	7.20	3.30	1.90	2.18
18	3.93	0.480	0.397	1.50	2.18	8.10	37.8	36.2	6.30	3.16	2.04	2.18
19	5.40	0.480	0.397	1.90	1.90	7.50	34.7	31.7	6.00	3.16	2.18	2.32
20	3.02	0.480	0.397	2.04	2.04	6.00	39.4	29.5	6.00	3.16	2.04	2.18
21	1.16	0.480	0.397	1.50	1.70	5.19	43.4	28.0	5.40	3.02	2.04	2.46
22	0.872	0.480	0.397	1.60	1.60	4.98	37.8	27.3	5.40	3.02	1.90	2.60
23	0.480	0.480	0.397	2.04	1.80	5.40	36.2	27.3	5.19	3.02	1.90	2.88
24	0.480	0.480	0.364	1.90	2.32	6.90	58.4	25.9	5.19	3.02	1.90	3.02
25	0.480	0.480	0.364	2.18	2.46	27.3	49.4	23.8	4.98	2.88	1.90	3.02
26	0.480	0.480	0.364	1.90	2.88	27.3	36.2	25.2	4.98	2.88	2.04	2.88
27	0.480	0.480	0.364	1.80	3.02	18.0	31.7	26.6	4.98	2.74	1.90	2.60
28	0.480	0.480	0.364	1.60	3.16	16.0	27.3	24.5	6.30	2.74	1.90	2.60
29	0.480	0.480	0.364	1.32	-----	15.6	30.2	20.5	6.90	2.88	2.04	2.74
30	0.480	0.480	0.364	1.24	-----	15.6	72.3	20.0	6.60	2.60	1.80	2.88
31	0.480	-----	0.364	1.50	-----	24.5	-----	20.5	-----	2.60	1.80	-----
Maks.	9.84	0.480	0.480	2.88	3.93	39.4	97.9	87.6	25.2	7.80	3.51	3.72
Min.	0.480	0.480	0.364	0.397	0.397	2.04	10.6	16.0	3.93	1.80	1.00	1.24
Ortalama	0.868	0.480	0.414	1.73	2.14	10.2	41.4	39.8	9.57	4.07	1.98	2.37
LT/SN/Km2	1.10	0.606	0.522	2.18	2.70	12.9	52.3	50.3	12.1	5.14	2.50	2.99
AKIM mm.	2.94	1.57	1.40	5.84	6.53	34.6	135.	135.	31.3	13.8	6.70	7.76
MİL. M3	2.33	1.24	1.11	4.62	5.17	27.4	107.	107.	24.8	10.9	5.31	6.15

SU YILI (2006) YILLIK TOPLAM AKIM 303.03 MİLYON M3 383 MM. 12.1 LT/SN/Km2

14. Yesilırmak Havzasi

D14A165 AKINOĞLU D. ÖZBARAKLI

YERİ : ÖZBARAKLI BELDESİNİN 5. KM GÜNEYİNDEDİR. 25 LİK PAFTADAKİ YERİ: G36-D1
36°3'50" Doğu - 40°41'30" Kuzey

YAĞIŞ ALANI : 27,50 km2 **YAKLAŞIK KOT :** 690 m

GÖZLEM SÜRESİ : 20.12.2004 - 30.09.2006

ORTALAMA AKIMLAR : Gözlem süresinde 0.202 m3/sn. (1 Yıllık) 2006 Su yılında 0.152 m3/sn.

ANLIK EN ÇOK VE EN AZ AKIMLAR:

2006 Su yılında anlık ençok akım	:	0.670 m3/sn	03.03.2006
2006 Su yılında anlık enaz akım	:	0.011 m3/sn	18.11.2005
Gözlem süresinde anlık ençok akım	:	0.670 m3/sn	03.03.2006
Gözlem süresinde anlık enaz akım	:	0.011 m3/sn	18.11.2005

1. Anahtar Eğrisi (Seviyeler cm olarak)

Seviye	Akım	Seviye	Akım	Seviye	Akım	Seviye	Akım
18	0.000	30	0.110	42	0.580	84	1.9
21	0.003	32	0.180	46	0.700	96	2.3
24	0.011	34	0.280	50	0.800	110	2.8
26	0.027	36	0.370	60	1.1	130	3.6
28	0.060	38	0.450	72	1.5	180	5.6

Akımlar 01 Ekim 2005 'den 30 Eylül 2006' a kadar m3/sn olarak

Gün	Ekim	Kasım	Aralık	Ocak	Şubat	Mart	Nisan	Mayıs	Haziran	Temmuz	Ağustos	Eylül
01	0.040	0.040	0.040	0.027	0.017	0.450	0.485	0.370	0.320	0.110	0.040	0.027
02	0.040	0.040	0.040	0.027	0.017	0.370	0.520	0.370	0.320	0.110	0.040	0.027
03	0.040	0.040	0.040	0.027	0.017	0.410	0.670	0.370	0.320	0.110	0.040	0.027
04	0.040	0.040	0.040	0.027	0.017	0.370	0.580	0.370	0.320	0.110	0.040	0.027
05	0.040	0.040	0.040	0.027	0.017	0.370	0.580	0.370	0.320	0.110	0.040	0.027
06	0.040	0.040	0.040	0.027	0.017	0.370	0.520	0.370	0.320	0.110	0.027	0.027
07	0.040	0.040	0.040	0.027	0.017	0.450	0.520	0.370	0.320	0.084	0.027	0.027
08	0.040	0.040	0.027	0.027	0.027	0.450	0.520	0.370	0.320	0.060	0.027	0.027
09	0.040	0.040	0.027	0.027	0.060	0.450	0.520	0.370	0.320	0.060	0.027	0.027
10	0.040	0.040	0.027	0.027	0.060	0.450	0.520	0.370	0.230	0.060	0.027	0.027
11	0.040	0.027	0.027	0.027	0.084	0.450	0.520	0.370	0.180	0.060	0.027	0.040
12	0.040	0.027	0.027	0.027	0.140	0.450	0.520	0.370	0.110	0.040	0.027	0.040
13	0.040	0.027	0.027	0.027	0.084	0.370	0.520	0.370	0.110	0.040	0.027	0.040
14	0.060	0.027	0.027	0.027	0.110	0.370	0.520	0.370	0.110	0.040	0.027	0.040
15	0.060	0.027	0.027	0.027	0.110	0.370	0.520	0.370	0.110	0.040	0.027	0.040
16	0.060	0.027	0.040	0.027	0.110	0.370	0.520	0.370	0.110	0.040	0.027	0.060
17	0.060	0.027	0.040	0.027	0.084	0.370	0.520	0.370	0.110	0.040	0.027	0.060
18	0.060	0.027	0.040	0.027	0.084	0.370	0.520	0.370	0.110	0.040	0.027	0.060
19	0.060	0.040	0.040	0.027	0.084	0.370	0.520	0.370	0.110	0.040	0.027	0.060
20	0.060	0.040	0.040	0.017	0.084	0.370	0.520	0.370	0.110	0.040	0.027	0.060
21	0.060	0.040	0.040	0.017	0.084	0.370	0.520	0.370	0.110	0.040	0.027	0.060
22	0.060	0.040	0.040	0.017	0.084	0.450	0.485	0.370	0.110	0.040	0.027	0.060
23	0.060	0.040	0.040	0.017	0.084	0.450	0.450	0.320	0.110	0.040	0.027	0.040
24	0.060	0.040	0.040	0.017	0.110	0.450	0.450	0.320	0.110	0.040	0.027	0.040
25	0.060	0.040	0.027	0.017	0.180	0.450	0.450	0.320	0.110	0.040	0.027	0.040
26	0.060	0.040	0.027	0.017	0.230	0.450	0.450	0.320	0.110	0.040	0.027	0.040
27	0.060	0.040	0.027	0.017	0.280	0.450	0.450	0.320	0.110	0.040	0.027	0.040
28	0.060	0.040	0.027	0.017	0.370	0.485	0.450	0.320	0.110	0.040	0.027	0.040
29	0.060	0.040	0.027	0.017	-----	0.485	0.450	0.320	0.110	0.040	0.027	0.040
30	0.040	0.040	0.027	0.017	-----	0.485	0.450	0.320	0.110	0.040	0.027	0.040
31	0.040	-----	0.027	0.017	-----	0.485	-----	0.320	-----	0.040	0.027	-----
Maks.	0.060	0.040	0.040	0.027	0.450	0.670	0.670	0.410	0.320	0.110	0.060	0.060
Min.	0.017	0.011	0.017	0.011	0.011	0.370	0.450	0.320	0.110	0.027	0.017	0.027
Ortalama	0.050	0.037	0.034	0.023	0.095	0.420	0.508	0.355	0.179	0.058	0.029	0.040
LT/SN/Km2	1.83	1.33	1.23	0.841	3.46	15.3	18.5	12.9	6.52	2.09	1.06	1.47
AKIM mm.	4.90	3.44	3.28	2.25	8.36	40.9	47.9	34.6	16.9	5.61	2.83	3.80
MİL. M3	0.135	0.095	0.090	0.062	0.230	1.12	1.32	0.952	0.465	0.154	0.078	0.105

SU YILI (2006) YILLIK TOPLAM AKIM 4.81 MİLYON M3 175 MM. 5.5 LT/SN/Km2

15

KIZILIRMAK HAVZASI

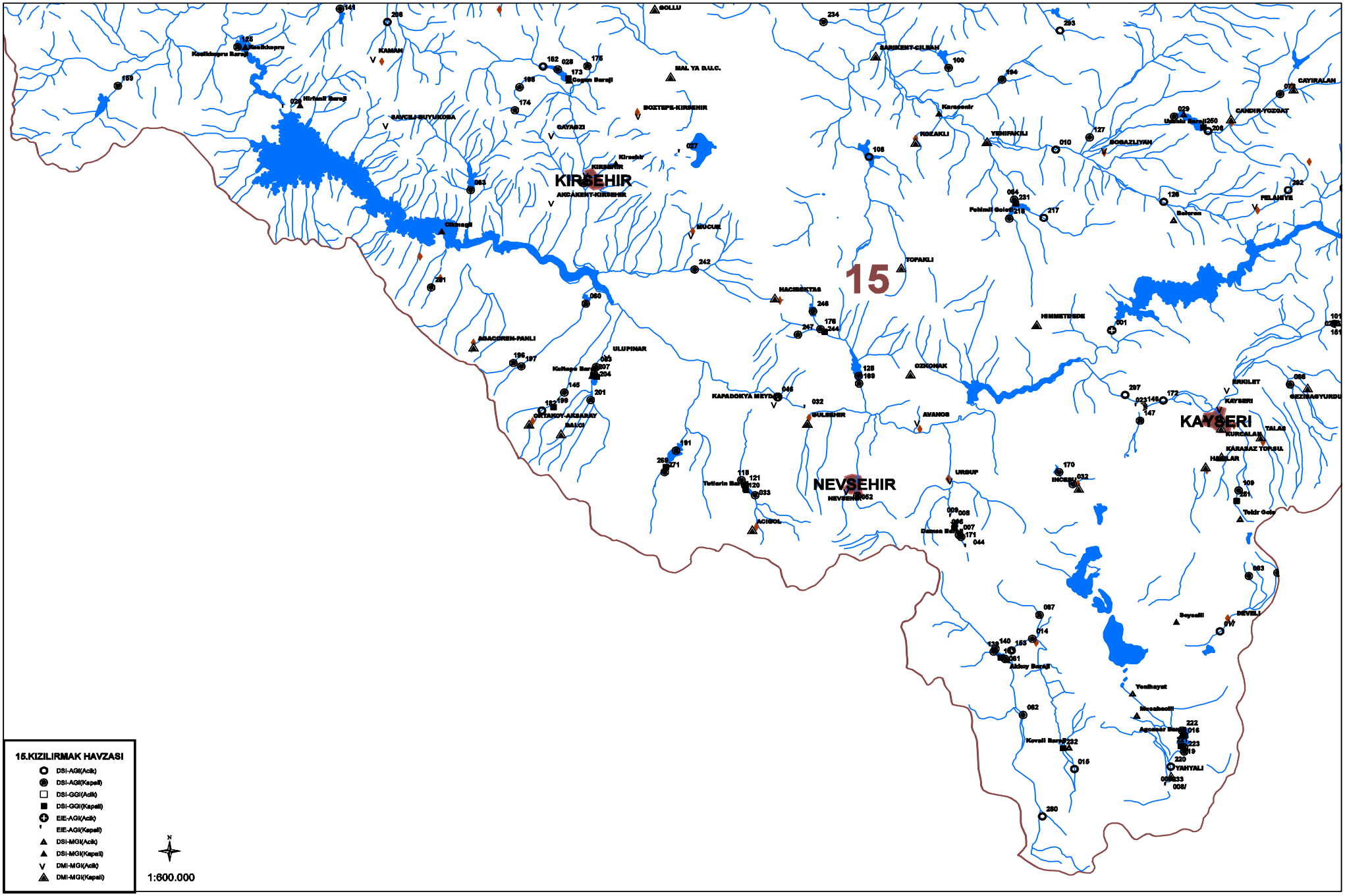
15
KIRSEHIR
NEVSEHIR
KAYSERI
15.KIZILIRMAK HAVZASI
DSI-AGI(Acik)
DSI-AGI(Kapali)
DSI-GGI(Acik)
DSI-GGI(Kapali)
EIE-AGI(Acik)
EIE-AGI(Kapali)
DSI-MGI(Acik)
DSI-MGI(Kapali)
DMI-MGI(Acik)
DMI-MGI(Kapali)
N
1:600.000

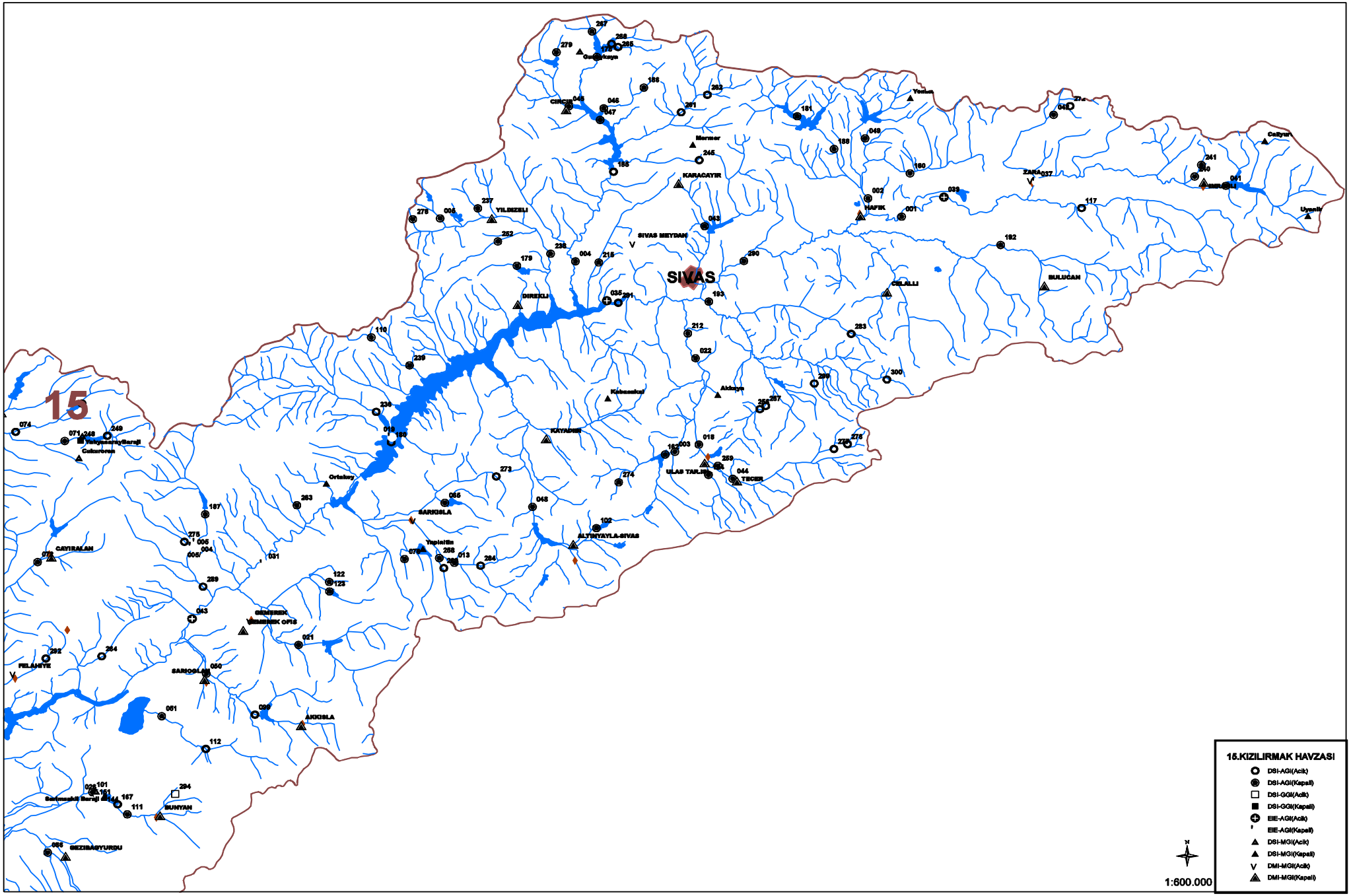
15
SIVAS
DIREKLI
YILDIZELI
KARACAYIR
HAFIK
ZARA
CELALLI
BULUCAN
KAYADERE
ULAS TARLA
TECER
ALTINYAYLA-SIVAS
SARIGSLA
Ortakoy
Kabasakal
Akkaya
Yenikent
Mermer
SIVAS MEYDAN
CIRCIR
Gurlevkaya
Yukyenicaybaraji
Cakirbeyli
CAYIRALAN
GEMEREK
GEMEREK OFIS
SARIOGLAN
AKKISLA
FELAHIYE
BUNYAN
GEZIBASYURDU
Sarimsakli Baraji
Yapraklin
Uyanik
Caltyar
1:600.000
15.KIZILIRMAK HAVZASI
DSI-AGI(Acik)
DSI-AGI(Kapali)
DSI-GGI(Acik)
DSI-GGI(Kapali)
EIE-AGI(Acik)
EIE-AGI(Kapali)
DSI-MGI(Acik)
DSI-MGI(Kapali)
DMI-MGI(Acik)
DMI-MGI(Kapali)

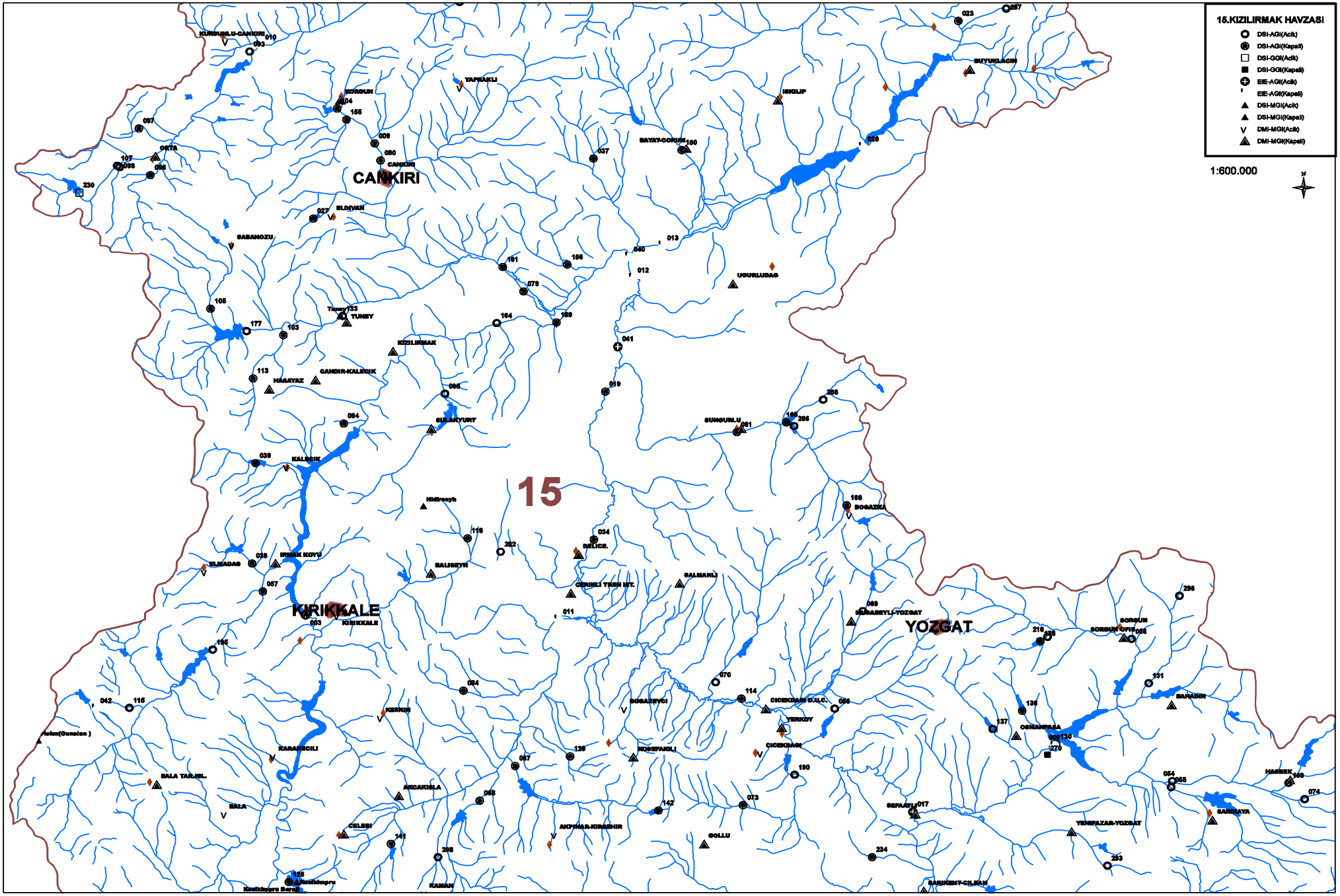
15.KIZILIRMAK HAVZASI
DSI-AGI(Acik)
DSI-AGI(Kapali)
DSI-GGI(Acik)
DSI-GGI(Kapali)
EIE-AGI(Acik)
EIE-AGI(Kapali)
DSI-MGI(Acik)
DSI-MGI(Kapali)
DMI-MGI(Acik)
DMI-MGI(Kapali)
1:600.000
N
15
CANKIRI
KIRIKKALE
YOZGAT
KURSUNLU-CANKIRI
KORGUN
YAPRAKLI
ISKILIP
SUYUKLACIN
BAYAT-CORUM
ORTA
ELDIVAN
SABANOZU
UGURLUDAG
TUNEY
KIZILIRMAK
CANDIR-KALECIK
HASAYAZ
SILAKYURT
SUNGURLU
KALECIK
BOGAZKIL
IRMAK KOYU
ELMADAG
BALISEYH
DELICE
SALMANLI
SORGUN
SORGUN CIFIR
SARADIN
OSMANPASA
CICEKDAGI D.M.C.
YERKOY
CICEKDAGI
BOGAZEVCI
KOSEFAKILI
KIRIKIN
KARAKECILI
BALA TARLISL.
BALA
ARCAKISLA
CILESI
AKPINAR-KIRSEHIR
GOLLU
SEFAATLI
YENIPAZAR-YOZGAT
SARIKAYA
HABEREK
SARIKENT-CILBAN
KAMAN
Kesikkopru Bendi
Kesikkopru
Kizilirmak(Gunelan)

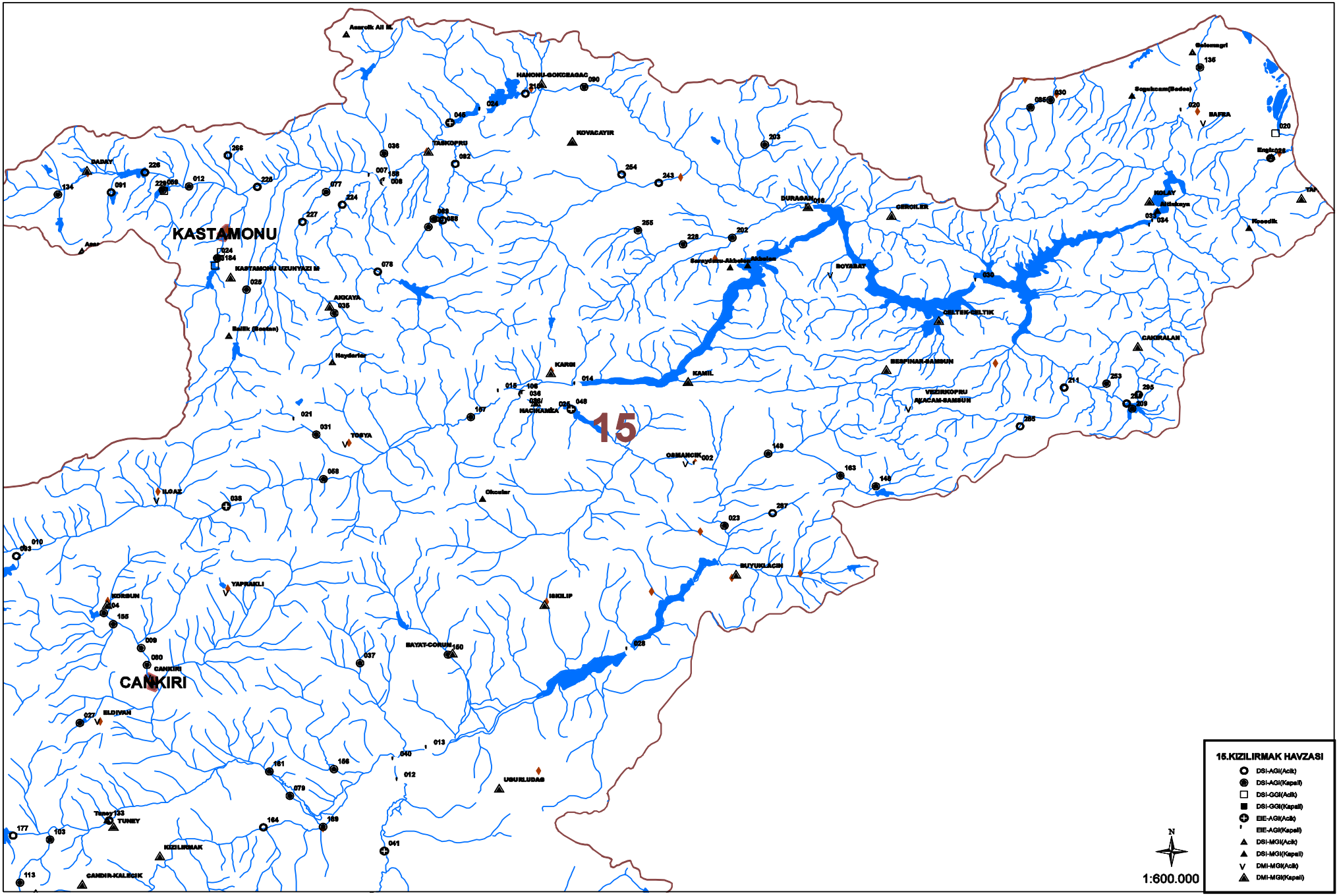
15
KASTAMONU
CANKIRI
15.KIZILIRMAK HAVZASI
DSI-AGI(Acik)
DSI-AGI(Kapali)
DSI-GGI(Acik)
DSI-GGI(Kapali)
EIE-AGI(Acik)
EIE-AGI(Kapali)
DSI-MGI(Acik)
DSI-MGI(Kapali)
DMI-MGI(Acik)
DMI-MGI(Kapali)
N
1:600.000

15. Kizilirmak Havzasi

D15A010 BOGAZLIYAN Ç. YESİLHİSAR

YERİ : **KAYSERİ BOĞAZLIYAN YOLUNUN 80.KM SİNDEN SOLA DÖNÜLEN BEKTAŞLI YOLUNUN 5.KM SİNDEKİ YEŞİLHİSAR KÖYÜNDEDİR.**
35°8'43" Doğu - 39°12'6" Kuzey

YAĞIŞ ALANI : **1825,00 km2** **YAKLAŞIK KOT : 1015 m**

GÖZLEM SÜRESİ : **15.07.1959 - 30.09.2006**

ORTALAMA AKIMLAR : **Gözlem süresinde 2.918 m3/sn. (45 Yıllık) 2006 Su yılında 0.580 m3/sn.**

ANLIK EN ÇOK VE EN AZ AKIMLAR:

2006 Su yılında anlık ençok akım	**:**	**4.44**	**m3/sn**	**21.04.2006**
2006 Su yılında anlık enaz akım	**:**	**0.000**	**m3/sn**	**01.10.2005**
Gözlem süresinde anlık ençok akım	**:**	**42.0**	**m3/sn**	**30.05.1968**
Gözlem süresinde anlık enaz akım	**:**	**0.000**	**m3/sn**	**09.10.2003**

11. Anahtar Eğrisi (Seviyeler cm olarak)

Seviye	Akım	Seviye	Akım	Seviye	Akım	Seviye	Akım
21	0.000	36	0.080	130	11.2	200	24.0
24	0.000	39	0.130	160	16.3	210	26.0
27	0.010	50	0.540	170	18.1	220	28.0
30	0.024	70	2.3	180	20.0	230	30.0
33	0.046	100	6.4	190	22.0	255	35.0

Akımlar 01 Ekim 2005 'den 30 Eylül 2006' a kadar m3/sn olarak

Gün	Ekim	Kasım	Aralık	Ocak	Şubat	Mart	Nisan	Mayıs	Haziran	Temmuz	Ağustos	Eylül
01	KURU	0.248	0.579	0.880	1.18	1.06	1.70	0.900	0.130	KURU	KURU	KURU
02	KURU	0.248	0.579	0.880	1.18	1.06	1.50	0.900	0.115	KURU	KURU	KURU
03	KURU	0.248	0.579	0.880	1.09	1.06	1.30	0.900	0.070	KURU	KURU	KURU
04	KURU	0.285	0.579	0.880	1.09	1.06	1.30	0.900	0.046	KURU	KURU	KURU
05	0.004	0.285	0.579	0.880	1.09	1.06	1.40	0.900	0.046	KURU	KURU	KURU
06	0.007	0.323	0.579	0.880	1.09	1.06	1.30	0.828	0.030	KURU	KURU	KURU
07	0.009	0.323	0.579	0.880	1.09	1.06	1.30	0.828	0.015	KURU	KURU	KURU
08	0.011	0.323	0.579	0.880	1.09	1.06	1.30	0.756	KURU	KURU	KURU	KURU
09	0.016	0.360	0.639	0.880	1.09	1.06	1.40	0.756	KURU	KURU	KURU	KURU
10	0.025	0.398	0.639	0.880	1.09	1.06	1.50	0.756	KURU	KURU	KURU	KURU
11	0.025	0.458	0.699	0.880	1.09	1.06	1.60	0.756	KURU	KURU	KURU	KURU
12	0.030	0.458	0.699	0.880	1.09	1.06	1.90	0.828	KURU	KURU	KURU	KURU
13	0.030	0.458	0.699	0.880	1.09	1.06	2.30	0.828	KURU	KURU	KURU	KURU
14	0.035	0.458	0.699	0.880	1.09	1.06	2.10	0.828	KURU	KURU	KURU	KURU
15	0.048	0.458	0.699	0.880	1.09	1.06	2.00	0.828	KURU	KURU	KURU	KURU
16	0.061	0.458	0.639	0.880	1.09	1.14	1.90	0.756	KURU	KURU	KURU	KURU
17	0.074	0.518	0.639	0.880	1.28	1.22	1.90	0.684	KURU	KURU	KURU	KURU
18	0.087	0.518	0.699	0.940	1.37	1.22	1.80	0.684	KURU	KURU	KURU	KURU
19	0.100	0.458	0.699	0.940	1.37	1.30	2.20	0.684	KURU	KURU	KURU	KURU
20	0.122	0.458	0.699	0.940	1.55	1.40	1.60	0.684	KURU	KURU	KURU	KURU
21	0.122	0.458	0.639	1.00	1.06	1.50	2.95	0.684	KURU	KURU	KURU	KURU
22	0.122	0.458	0.699	1.09	1.06	1.70	2.43	0.684	KURU	KURU	KURU	KURU
23	0.122	0.458	0.699	1.09	1.06	1.70	2.20	0.684	KURU	KURU	KURU	KURU
24	0.122	0.458	0.699	1.18	1.06	1.70	2.10	0.612	KURU	KURU	KURU	KURU
25	0.122	0.458	0.699	1.18	1.06	1.70	1.90	0.540	KURU	KURU	KURU	KURU
26	0.144	0.458	0.699	1.18	1.06	1.70	1.80	0.448	KURU	KURU	KURU	KURU
27	0.188	0.458	0.699	1.18	1.06	1.70	1.80	0.356	KURU	KURU	KURU	KURU
28	0.188	0.518	0.759	1.18	1.06	1.70	1.30	0.310	KURU	KURU	KURU	KURU
29	0.188	0.579	0.880	1.18	-----	1.70	1.14	0.160	KURU	KURU	KURU	KURU
30	0.210	0.579	0.880	1.18	-----	1.70	0.900	0.130	KURU	KURU	KURU	KURU
31	0.248	-----	0.880	1.18	-----	1.70	-----	0.130	-----	KURU	KURU	-----
Maks.	0.398	0.819	1.00	1.37	1.55	2.00	4.44	0.900	0.130	KURU	KURU	KURU
Min.	KURU	0.248	0.579	0.880	1.06	1.06	0.900	0.130	KURU	KURU	KURU	KURU
Ortalama	0.079	0.421	0.678	0.981	1.13	1.31	1.73	0.668	0.015	KURU	KURU	KURU
LT/SN/Km2	0.043	0.231	0.371	0.537	0.620	0.719	0.946	0.366	0.008	0.000	0.000	0.000
AKIM mm.	0.116	0.598	0.995	1.44	1.50	1.93	2.45	0.981	0.021	0.000	0.000	0.000
MİL. M3	0.213	1.09	1.82	2.63	2.74	3.51	4.48	1.79	0.039	0.000	0.000	0.000

SU YILI (2006) YILLIK TOPLAM AKIM 18.31 MİLYON M3 10 MM. 0.3 LT/SN/Km2

15. Kizilırmak Havzasi

D15A015 DÜNDARLI SUYU HACIBEYLİ

YERİ : **YEŞİLHİSAR NİĞDE YOLUNUN 12.KM SİNDEN SOLA DÖNEN KÖY YOLUNUN 1.KM SİNDEDİR.**
35°9'58" Doğu - 38°7'51" Kuzey

YAĞIŞ ALANI : **133,00 km2** **YAKLAŞIK KOT : 1215 m**

GÖZLEM SÜRESİ : **01.04.1959 - 30.09.2006**

ORTALAMA AKIMLAR : **Gözlem süresinde 0.962 m3/sn. (45 Yıllık) 2006 Su yılında 0.536 m3/sn.**

ANLIK EN ÇOK VE EN AZ AKIMLAR:

2006 Su yılında anlık ençok akım	**:**	**3.32**	**m3/sn**	**04.05.2006**
2006 Su yılında anlık enaz akım	**:**	**0.075**	**m3/sn**	**01.06.2006**
Gözlem süresinde anlık ençok akım	**:**	**32.0**	**m3/sn**	**07.05.1969**
Gözlem süresinde anlık enaz akım	**:**	**0.000**	**m3/sn**	**22.08.1979**

31. Anahtar Eğrisi (Seviyeler cm olarak)

Seviye	Akım	Seviye	Akım	Seviye	Akım	Seviye	Akım
4	0.013	12	0.150	40	2.3	90	13.6
6	0.023	15	0.270	50	4.0	92	14.0
8	0.051	20	0.500	60	6.2	100	16.4
10	0.096	25	0.800	70	9.1	110	19.2
11	0.120	30	1.2	80	11.3	115	20.7

Akımlar 01 Ekim 2005 'den 30 Eylül 2006' a kadar m3/sn olarak

Gün	Ekim	Kasım	Aralık	Ocak	Şubat	Mart	Nisan	Mayıs	Haziran	Temmuz	Ağustos	Eylül
01	0.120	0.362	0.408	0.270	0.230	0.316	0.560	2.09	1.55	0.120	0.075	0.075
02	0.190	0.362	0.408	0.270	0.230	0.316	0.680	2.09	1.55	0.120	0.075	0.075
03	0.230	0.362	0.408	0.270	0.230	0.316	0.800	2.47	1.55	0.120	0.075	0.075
04	0.316	0.362	0.408	0.270	0.230	0.316	1.06	2.81	1.55	0.120	0.075	0.075
05	0.316	0.362	0.408	0.270	0.230	0.316	1.34	2.64	1.55	0.120	0.075	0.075
06	0.316	0.362	0.408	0.270	0.230	0.270	1.34	2.30	1.55	0.120	0.075	0.075
07	0.316	0.362	0.408	0.316	0.230	0.270	1.34	2.09	1.55	0.120	0.075	0.075
08	0.316	0.362	0.408	0.316	0.230	0.270	1.34	2.09	1.55	0.120	0.075	0.075
09	0.316	0.362	0.408	0.316	0.230	0.316	1.55	1.87	1.55	0.120	0.075	0.075
10	0.316	0.362	0.408	0.316	0.230	0.316	1.87	1.66	1.55	0.120	0.075	0.075
11	0.316	0.362	0.408	0.316	0.230	0.316	2.09	1.55	1.55	0.120	0.075	0.075
12	0.316	0.362	0.408	0.316	0.230	0.316	1.66	1.55	1.55	0.120	0.075	0.096
13	0.316	0.362	0.408	0.316	0.230	0.270	1.87	1.55	1.55	0.120	0.075	0.096
14	0.316	0.362	0.408	0.316	0.230	0.270	2.09	1.55	1.55	0.120	0.075	0.096
15	0.316	0.362	0.408	0.316	0.230	0.270	1.87	1.55	1.55	0.120	0.075	0.096
16	0.316	0.362	0.408	0.316	0.230	0.270	1.77	1.55	0.408	0.120	0.075	0.096
17	0.316	0.362	0.408	0.316	0.230	0.270	1.77	1.55	0.075	0.120	0.075	0.096
18	0.362	0.362	0.408	0.270	0.230	0.316	1.55	1.55	0.075	0.120	0.075	0.096
19	0.362	0.362	0.408	0.270	0.230	0.362	1.34	1.55	0.075	0.075	0.075	0.096
20	0.362	0.362	0.408	0.270	0.230	0.362	1.34	1.55	0.075	0.075	0.075	0.096
21	0.362	0.362	0.408	0.270	0.230	0.362	1.55	1.55	0.075	0.075	0.075	0.096
22	0.362	0.362	0.408	0.270	0.230	0.362	1.44	1.55	0.075	0.075	0.075	0.096
23	0.362	0.362	0.408	0.270	0.230	0.362	1.44	1.55	0.075	0.075	0.075	0.096
24	0.362	0.362	0.408	0.270	0.230	0.408	1.55	1.55	0.075	0.075	0.075	0.096
25	0.362	0.362	0.408	0.270	0.270	0.408	2.30	1.55	0.075	0.075	0.075	0.120
26	0.362	0.362	0.316	0.270	0.316	0.408	2.19	1.55	0.075	0.075	0.075	0.120
27	0.362	0.362	0.316	0.270	0.316	0.454	2.30	1.55	0.075	0.075	0.075	0.120
28	0.362	0.362	0.316	0.270	0.316	0.454	2.19	1.55	0.075	0.075	0.075	0.120
29	0.362	0.362	0.316	0.270	-----	0.454	2.09	1.55	0.190	0.075	0.075	0.120
30	0.362	0.362	0.270	0.270	-----	0.454	2.30	1.55	0.316	0.075	0.075	0.120
31	0.362	-----	0.270	0.270	-----	0.454	-----	1.55	-----	0.075	0.075	-----
Maks.	0.362	0.362	0.408	0.316	0.316	0.454	2.98	3.32	1.55	0.190	0.075	0.120
Min.	0.120	0.362	0.270	0.270	0.230	0.270	0.560	1.55	0.075	0.075	0.075	0.075
Ortalama	0.324	0.362	0.387	0.286	0.241	0.343	1.62	1.76	0.835	0.101	0.075	0.093
LT/SN/Km2	2.43	2.72	2.91	2.15	1.81	2.58	12.2	13.3	6.28	0.760	0.564	0.700
AKIM mm.	6.52	7.05	7.80	5.77	4.38	6.90	31.6	35.5	16.3	2.04	1.51	1.81
MİL. M3	0.867	0.938	1.04	0.767	0.582	0.918	4.20	4.72	2.17	0.271	0.201	0.241

SU YILI (2006) YILLIK TOPLAM AKIM 16.92 MİLYON M3 127 MM. 4.0 LT/SN/Km2

15. Kizilırmak Havzasi

D15A017 DEVELİ SUYU GEDİNE

YERİ : **DEVELİ YAHYALI YOLUNUN 1.KM SİNDEKİ KÖPRÜNÜN 200M. MEMBASINDADIR.**
35°28'26" Doğu - 38°21'57" Kuzey

YAĞIŞ ALANI : **164,00 km2** **YAKLAŞIK KOT : 1145 m**

GÖZLEM SÜRESİ : **01.04.1959 - 30.09.2006**

ORTALAMA AKIMLAR : **Gözlem süresinde 0.123 m3/sn. (38 Yıllık) 2006 Su yılında 0.015 m3/sn.**

ANLIK EN ÇOK VE EN AZ AKIMLAR:

2006 Su yılında anlık ençok akım	:	**0.664**	**m3/sn**	**01.04.2006**
2006 Su yılında anlık enaz akım	:	**0.000**	**m3/sn**	**01.10.2005**
Gözlem süresinde anlık ençok akım	:	**12.3**	**m3/sn**	**06.04.2000**
Gözlem süresinde anlık enaz akım	:	**0.000**	**m3/sn**	**01.10.1974**

14. Anahtar Eğrisi (Seviyeler cm olarak)

Seviye	Akım	Seviye	Akım	Seviye	Akım	Seviye	Akım
1	0.000	6	0.002	26	1.4	71	5.8
2	0.000	7	0.019	31	1.8	81	6.8
3	0.000	11	0.160	41	2.8	91	7.5
4	0.000	16	0.500	51	3.9		
5	0.000	21	0.910	61	4.8		

Akımlar 01 Ekim 2005 'den 30 Eylül 2006' a kadar m3/sn olarak

Gün	Ekim	Kasım	Aralık	Ocak	Şubat	Mart	Nisan	Mayıs	Haziran	Temmuz	Ağustos	Eylül
01	KURU	KURU	KURU	0.054	0.054	0.002	0.019	0.002	KURU	KURU	KURU	KURU
02	KURU	KURU	KURU	0.054	0.054	0.002	0.228	0.019	KURU	KURU	KURU	KURU
03	KURU	KURU	KURU	0.054	0.054	0.002	0.125	0.019	KURU	KURU	KURU	KURU
04	KURU	KURU	KURU	0.054	0.054	0.002	0.125	0.019	KURU	KURU	KURU	KURU
05	KURU	KURU	KURU	0.054	0.054	0.002	0.125	0.019	KURU	KURU	KURU	KURU
06	KURU	KURU	KURU	0.054	0.054	0.002	0.090	0.019	KURU	KURU	KURU	KURU
07	KURU	KURU	KURU	0.054	0.054	0.002	0.090	0.019	KURU	KURU	KURU	KURU
08	KURU	KURU	KURU	0.054	0.054	0.002	0.090	0.019	KURU	KURU	KURU	KURU
09	KURU	KURU	0.019	0.054	0.054	0.002	0.054	0.019	KURU	KURU	KURU	KURU
10	KURU	KURU	0.019	0.054	0.054	0.002	0.160	0.002	KURU	KURU	KURU	KURU
11	KURU	KURU	0.019	0.054	0.054	0.002	0.160	KURU	KURU	KURU	KURU	KURU
12	KURU	KURU	0.019	0.054	0.054	0.002	0.090	KURU	KURU	KURU	KURU	KURU
13	KURU	KURU	0.019	0.054	0.054	KURU	0.125	KURU	KURU	KURU	KURU	KURU
14	KURU	KURU	0.019	0.054	0.054	KURU	0.125	KURU	KURU	KURU	KURU	KURU
15	KURU	KURU	0.019	0.054	0.054	KURU	0.019	KURU	KURU	KURU	KURU	KURU
16	KURU	KURU	0.054	0.054	0.019	KURU	0.019	KURU	KURU	KURU	KURU	KURU
17	KURU	KURU	0.054	0.054	0.019	KURU	0.019	KURU	KURU	KURU	KURU	KURU
18	KURU	KURU	0.054	0.054	0.002	KURU	0.019	KURU	KURU	KURU	KURU	KURU
19	KURU	KURU	0.054	0.054	0.002	KURU	0.019	KURU	KURU	KURU	KURU	KURU
20	KURU	KURU	0.054	0.054	0.002	KURU	0.002	KURU	KURU	KURU	KURU	KURU
21	KURU	KURU	0.054	0.054	0.019	KURU	0.002	KURU	KURU	KURU	KURU	KURU
22	KURU	KURU	0.054	0.054	0.002	KURU	0.002	KURU	KURU	KURU	KURU	KURU
23	KURU	KURU	0.054	0.054	0.002	0.002	0.002	KURU	KURU	KURU	KURU	KURU
24	KURU	KURU	0.054	0.054	0.002	0.002	0.002	KURU	KURU	KURU	KURU	KURU
25	KURU	KURU	0.054	0.054	0.002	0.002	0.002	KURU	KURU	KURU	KURU	KURU
26	KURU	KURU	0.054	0.054	0.002	0.002	0.002	KURU	KURU	KURU	KURU	KURU
27	KURU	KURU	0.054	0.054	0.002	0.002	0.002	KURU	KURU	KURU	KURU	KURU
28	KURU	KURU	0.054	0.054	0.002	0.002	0.002	KURU	KURU	KURU	KURU	KURU
29	KURU	KURU	0.054	0.054	-----	0.002	0.002	KURU	KURU	KURU	KURU	KURU
30	KURU	KURU	0.054	0.054	-----	0.002	0.002	KURU	KURU	KURU	KURU	KURU
31	KURU	-----	0.054	0.054	-----	0.002	-----	KURU	-----	KURU	KURU	-----
Maks.	KURU	KURU	0.364	0.054	0.054	0.002	0.664	0.500	KURU	KURU	KURU	KURU
Min.	KURU	KURU	KURU	0.054	0.002	KURU	0.002	KURU	KURU	KURU	KURU	KURU
Ortalama	KURU	KURU	0.032	0.054	0.032	0.001	0.057	0.005	KURU	KURU	KURU	KURU
LT/SN/Km2	0.000	0.000	0.196	0.329	0.193	0.008	0.350	0.031	0.000	0.000	0.000	0.000
AKIM mm.	0.000	0.000	0.525	0.882	0.467	0.022	0.908	0.082	0.000	0.000	0.000	0.000
MİL. M3	0.000	0.000	0.086	0.145	0.077	0.004	0.149	0.013	0.000	0.000	0.000	0.000

SU YILI (2006) YILLIK TOPLAM AKIM 0.47 MİLYON M3 3 MM. 0.1 LT/SN/Km2

15. Kizilirmak Havzasi

D15A026 ENGİZ D. BALLICA

YERİ : **SAMSUN-BAFRA KARAYOLUNUN 33. KM 19 MAYIS İLÇESİNDEN SOLA AYRILAN ASFALT YOLUN 3 KM SİNDEDİR. 25 LİK PAFTADAKİ YERİ: F36-A1**
36°4'3" Doğu - 41°29'11" Kuzey

YAĞIŞ ALANI : **151,40 km2** **YAKLAŞIK KOT : 15 m**

GÖZLEM SÜRESİ : **27.07.1967 - 30.09.2006**

ORTALAMA AKIMLAR : **Gözlem süresinde 2.538 m3/sn. (35 Yıllık) 2006 Su yılında 2.601 m3/sn.**

ANLIK EN ÇOK VE EN AZ AKIMLAR:

2006 Su yılında anlık ençok akım	**:**	**62.0**	**m3/sn**	**04.11.2005**
2006 Su yılında anlık enaz akım	**:**	**0.001**	**m3/sn**	**18.09.2006**
Gözlem süresinde anlık ençok akım	**:**	**350.**	**m3/sn**	**13.05.1997**
Gözlem süresinde anlık enaz akım	**:**	**0.000**	**m3/sn**	**07.04.1979**

30. Anahtar Eğrisi (Seviyeler cm olarak)

Seviye	Akım	Seviye	Akım	Seviye	Akım	Seviye	Akım
1	0.000	21	0.580	71	9.2	201	127.
4	0.008	26	0.960	81	13.0	211	140.
7	0.042	36	2.0	111	29.0	251	215.
10	0.100	49	4.0	141	54.0	301	330.
15	0.270	59	6.0	171	86.0	351	480.

Akımlar 01 Ekim 2005 'den 30 Eylül 2006' a kadar m3/sn olarak

Gün	Ekim	Kasım	Aralık	Ocak	Şubat	Mart	Nisan	Mayıs	Haziran	Temmuz	Ağustos	Eylül
01	1.03	8.90	0.720	3.30	2.00	9.90	4.40	0.880	1.20	0.720	0.058	0.017
02	0.960	8.60	0.720	2.28	2.14	6.95	4.00	0.880	0.473	0.650	0.058	0.527
03	0.800	8.90	0.580	1.64	3.00	7.18	3.83	0.800	0.420	2.70	0.042	0.130
04	2.56	20.6	0.580	1.52	3.65	5.60	3.48	0.650	0.420	1.03	0.042	0.017
05	3.30	20.6	0.580	1.52	3.48	3.65	3.15	0.650	0.360	0.527	0.028	0.008
06	2.56	15.8	0.580	1.52	5.00	3.83	3.00	0.650	0.270	0.473	0.028	0.008
07	2.28	15.0	0.473	1.64	7.70	4.60	2.70	0.650	0.270	0.315	0.028	0.100
08	2.28	26.0	0.360	2.85	4.80	4.80	4.00	0.650	0.270	0.230	0.017	0.042
09	2.14	8.00	0.360	2.70	5.20	4.00	7.18	0.650	0.270	0.230	0.017	0.008
10	2.14	1.10	0.360	2.42	5.00	2.70	9.20	0.527	1.52	0.160	0.008	0.008
11	2.14	0.800	1.64	2.42	20.0	2.28	12.5	0.527	0.960	0.100	0.008	0.077
12	2.14	0.800	2.42	4.00	9.67	2.14	3.65	0.527	0.960	0.077	0.008	0.473
13	2.42	0.800	1.52	5.80	5.40	2.42	1.52	0.527	0.880	0.058	0.008	0.130
14	2.70	0.800	1.10	3.30	4.00	2.56	1.40	1.52	0.527	0.058	0.008	0.077
15	2.70	0.800	0.880	2.42	3.65	2.56	1.20	1.30	0.880	0.058	0.008	0.042
16	2.70	0.360	0.880	2.28	3.15	2.42	1.10	0.960	0.720	0.042	0.003	0.028
17	4.40	0.230	0.960	2.28	2.85	2.42	0.880	1.20	0.580	0.017	0.003	0.017
18	4.20	0.230	0.960	2.85	10.7	2.42	0.880	6.95	0.360	0.042	0.003	0.008
19	3.83	0.230	0.880	3.00	15.0	5.80	0.880	4.60	0.360	0.017	0.003	0.003
20	5.80	0.270	4.00	6.00	12.0	5.40	0.880	3.30	0.270	0.017	0.003	0.003
21	7.18	13.0	1.88	4.40	9.67	4.80	0.880	2.70	0.230	0.017	0.003	0.008
22	7.18	4.40	1.40	4.40	7.70	5.20	0.880	2.14	0.230	0.017	0.003	1.88
23	8.00	2.14	1.20	4.60	7.18	4.20	0.880	1.88	0.230	0.017	0.003	0.580
24	8.00	1.88	1.20	4.00	7.40	2.85	1.40	1.64	0.230	0.017	0.003	0.420
25	6.73	2.42	1.20	3.65	13.8	8.30	2.56	1.64	0.190	0.017	0.003	0.360
26	6.73	3.83	1.20	3.00	13.0	6.25	1.76	1.40	0.130	0.008	0.003	2.56
27	6.73	2.70	1.20	2.00	10.7	5.80	1.40	2.70	0.058	0.008	0.003	0.650
28	6.50	1.64	1.64	1.76	8.00	6.73	1.03	2.42	0.058	0.017	0.003	0.270
29	6.50	1.20	3.00	1.52	-----	6.50	0.960	1.76	0.077	0.028	0.003	0.130
30	7.18	0.960	3.15	1.52	-----	5.60	0.880	1.52	1.40	0.190	0.003	0.077
31	9.20	-----	3.15	1.76	-----	4.60	-----	1.40	-----	0.077	0.003	-----
Maks.	9.90	62.0	6.73	9.43	31.8	20.6	16.6	10.7	4.60	5.60	0.100	4.60
Min.	0.720	0.130	0.315	1.52	2.00	2.14	0.880	0.270	0.017	0.008	0.003	0.001
Ortalama	4.29	5.77	1.32	2.85	7.35	4.66	2.75	1.60	0.493	0.256	0.013	0.289
LT/SN/Km2	28.3	38.1	8.69	18.8	48.6	30.8	18.2	10.6	3.26	1.69	0.088	1.91
AKIM mm.	75.9	98.7	23.3	50.4	117.	82.4	47.1	28.3	8.45	4.53	0.236	4.94
MİL. M3	11.5	14.9	3.52	7.63	17.8	12.5	7.12	4.29	1.28	0.685	0.036	0.748

SU YILI (2006) YILLIK TOPLAM AKIM 82.01 MİLYON M3 542 MM. 17.2 LT/SN/Km2

15. Kizilirmak Havzasi

D15A039 KOZAYAĞI DERESİ KOZAYAĞI

YERİ : **ANKARA-ÇANKIRI YOLUNUN 53.KM SINDEN SAGA AYRILAN KOZAYAGI KÖYÜ YOLUNUN 2. KM SINDEKI KOPRUNUN MANSABINDADIR.**
33°15'55" Doğu - 40°7'40" Kuzey

YAĞIŞ ALANI : **49.92 km2** **YAKLAŞIK KOT : 1100 m**

GÖZLEM SÜRESİ : **01.10.1967 - 30.09.2006**

ORTALAMA AKIMLAR : **Gözlem süresinde 0.375 m3/sn. (6 Yıllık) 2006 Su yılında 0.172 m3/sn.**

ANLIK EN ÇOK VE EN AZ AKIMLAR:

2006 Su yılında anlık ençok akım	**:**	**1.80**	**m3/sn**	**03.03.2006**
2006 Su yılında anlık enaz akım	**:**	**0.005**	**m3/sn**	**03.02.2006**
Gözlem süresinde anlık ençok akım	**:**	**56.0**	**m3/sn**	**12.03.1968**
Gözlem süresinde anlık enaz akım	**:**	**0.001**	**m3/sn**	**01.10.1967**

2. Anahtar Eğrisi (Seviyeler cm olarak)

Seviye	Akım	Seviye	Akım	Seviye	Akım
30	0.002	35	0.021	40	0.140
31	0.003	36	0.032	45	0.430
32	0.005	37	0.052	50	1.0
33	0.009	38	0.074	55	1.8
34	0.014	39	0.100	60	3.0

Akımlar 01 Ekim 2005 'den 30 Eylül 2006' a kadar m3/sn olarak

Gün	Ekim	Kasım	Aralık	Ocak	Şubat	Mart	Nisan	Mayıs	Haziran	Temmuz	Ağustos	Eylül
01	0.052	0.032	0.052	0.052	0.032	0.658	0.658	0.256	0.140	0.074	0.021	0.014
02	0.052	0.032	0.052	0.052	0.009	0.430	0.658	0.256	0.140	0.074	0.021	0.032
03	0.052	0.032	0.052	0.052	0.005	1.00	0.658	0.256	0.140	0.074	0.021	0.032
04	0.052	0.032	0.052	0.052	0.014	0.544	0.658	0.256	0.140	0.052	0.021	0.021
05	0.052	0.032	0.052	0.052	0.014	0.430	0.544	0.256	0.140	0.052	0.021	0.021
06	0.052	0.032	0.052	0.052	0.021	0.372	0.544	0.256	0.100	0.052	0.021	0.021
07	0.052	0.032	0.052	0.052	0.052	0.314	0.544	0.256	0.140	0.032	0.021	0.021
08	0.052	0.032	0.052	0.052	0.074	0.372	0.658	0.256	0.198	0.032	0.014	0.014
09	0.052	0.032	0.052	0.052	0.074	0.430	0.886	0.256	0.198	0.032	0.014	0.014
10	0.052	0.032	0.052	0.052	0.074	0.430	1.32	0.256	0.198	0.052	0.014	0.014
11	0.052	0.032	0.052	0.052	0.256	0.372	1.64	0.256	0.198	0.052	0.021	0.014
12	0.052	0.032	0.052	0.052	0.256	0.372	1.64	0.256	0.198	0.052	0.014	0.014
13	0.052	0.032	0.052	0.052	0.140	0.430	1.32	0.256	0.198	0.032	0.021	0.014
14	0.052	0.032	0.052	0.052	0.140	0.886	1.00	0.256	0.198	0.032	0.014	0.014
15	0.052	0.032	0.052	0.052	0.140	0.658	0.772	0.256	0.198	0.032	0.014	0.014
16	0.052	0.032	0.052	0.052	0.100	0.544	0.544	0.256	0.198	0.032	0.014	0.014
17	0.052	0.032	0.052	0.052	0.052	0.544	0.430	0.314	0.140	0.032	0.021	0.021
18	0.052	0.032	0.052	0.052	0.074	0.544	0.430	0.314	0.100	0.032	0.021	0.021
19	0.052	0.032	0.052	0.052	0.256	0.544	0.372	0.314	0.100	0.032	0.014	0.021
20	0.052	0.032	0.052	0.074	0.256	0.658	0.372	0.314	0.100	0.032	0.014	0.021
21	0.052	0.032	0.052	0.052	0.314	0.544	0.372	0.256	0.074	0.032	0.014	0.021
22	0.052	0.032	0.052	0.074	0.314	0.544	0.314	0.256	0.052	0.032	0.014	0.021
23	0.052	0.032	0.052	0.074	0.314	0.544	0.314	0.256	0.052	0.032	0.014	0.021
24	0.052	0.032	0.052	0.074	0.256	0.544	0.314	0.256	0.052	0.032	0.014	0.021
25	0.052	0.032	0.052	0.074	0.372	0.772	0.314	0.256	0.052	0.032	0.014	0.021
26	0.052	0.052	0.052	0.052	0.772	0.886	0.314	0.256	0.032	0.032	0.014	0.032
27	0.052	0.052	0.052	0.052	0.886	0.772	0.314	0.256	0.052	0.021	0.014	0.032
28	0.052	0.052	0.052	0.052	0.658	0.772	0.256	0.256	0.052	0.021	0.014	0.032
29	0.052	0.052	0.052	0.052	-----	0.772	0.256	0.256	0.100	0.032	0.014	0.032
30	0.052	0.052	0.052	0.052	-----	0.772	0.256	0.198	0.100	0.032	0.014	0.032
31	0.052	-----	0.052	0.052	-----	0.772	-----	0.140	-----	0.021	0.014	-----
Maks.	0.052	0.052	0.074	0.100	1.48	1.80	1.80	0.372	0.256	0.100	0.052	0.052
Min.	0.032	0.032	0.032	0.052	0.005	0.314	0.198	0.140	0.032	0.021	0.014	0.014
Ortalama	0.052	0.035	0.052	0.056	0.212	0.588	0.622	0.258	0.126	0.039	0.016	0.021
LT/SN/Km2	1.04	0.708	1.04	1.11	4.24	11.8	12.5	5.17	2.52	0.779	0.330	0.425
AKIM mm.	2.79	1.83	2.79	2.98	10.3	31.5	32.3	13.8	6.54	2.09	0.884	1.10
MİL. M3	0.139	0.092	0.139	0.149	0.512	1.57	1.61	0.691	0.327	0.104	0.044	0.055

SU YILI (2006) YILLIK TOPLAM AKIM 5.43 MİLYON M3 109 MM. 3.5 LT/SN/Km2

15. Kizilirmak Havzasi

D15A054 BÜYÜK KANAK ÇAYI KADILI

YERİ : 1979SORGUN-SARIKAYA İLÇELERİ YOLUNUN 42.KM SİNDEKİ KADILI KÖYÜNDEDİR
35°17'55" Doğu - 39°33'5" Kuzey

YAĞIŞ ALANI : 748,00 km2 **YAKLAŞIK KOT :** 901 m

GÖZLEM SÜRESİ : 15.10.1963 - 30.09.2006

ORTALAMA AKIMLAR : Gözlem süresinde 1.000 m3/sn. (38 Yıllık) 2006 Su yılında 0.339 m3/sn.

ANLIK EN ÇOK VE EN AZ AKIMLAR:

2006 Su yılında anlık ençok akım	:	3.80	m3/sn	28.05.2006
2006 Su yılında anlık enaz akım	:	0.000	m3/sn	05.07.2006
Gözlem süresinde anlık ençok akım	:	39.0	m3/sn	04.05.1980
Gözlem süresinde anlık enaz akım	:	0.000	m3/sn	31.07.1974

13. Anahtar Eğrisi (Seviyeler cm olarak)

Seviye	Akım	Seviye	Akım	Seviye	Akım	Seviye	Akım
35	0.010	70	1.4	120	4.9	170	8.6
45	0.270	80	2.0	130	5.6	180	9.3
50	0.490	90	2.6	140	6.2	190	10.0
55	0.700	100	3.4	150	7.0	200	11.0
60	0.960	110	4.2	160	7.8	250	16.0

Akımlar 01 Ekim 2005 'den 30 Eylül 2006' a kadar m3/sn olarak

Gün	Ekim	Kasım	Aralık	Ocak	Şubat	Mart	Nisan	Mayıs	Haziran	Temmuz	Ağustos	Eylül
01	0.002	0.334	0.592	0.592	0.064	0.064	0.700	1.06	0.636	0.033	KURU	KURU
02	0.002	0.334	0.592	0.592	0.064	0.064	0.700	1.01	0.376	0.022	KURU	KURU
03	0.003	0.334	0.592	0.592	0.082	0.082	0.700	2.10	0.250	0.008	KURU	KURU
04	0.005	0.376	0.592	0.592	0.082	0.082	0.700	2.10	0.225	0.002	KURU	KURU
05	0.005	0.418	0.592	0.592	0.082	0.082	0.700	1.95	0.225	KURU	KURU	KURU
06	0.006	0.418	0.592	0.680	0.082	0.082	0.700	1.85	0.225	KURU	KURU	KURU
07	0.006	0.418	0.592	0.680	0.100	0.100	0.700	1.85	0.175	KURU	KURU	KURU
08	0.008	0.418	0.592	0.202	0.100	0.100	0.700	1.85	0.150	KURU	KURU	KURU
09	0.008	0.418	0.592	0.168	0.134	0.134	0.700	1.85	0.150	KURU	KURU	KURU
10	0.008	0.418	0.592	0.168	0.134	0.134	0.700	1.85	0.150	KURU	KURU	KURU
11	0.008	0.418	0.592	0.134	0.134	0.134	0.700	1.75	0.150	KURU	KURU	KURU
12	0.013	0.418	0.592	0.100	0.134	0.134	0.752	1.60	0.130	KURU	KURU	KURU
13	0.022	0.418	0.592	0.082	0.168	0.168	0.752	1.55	0.096	KURU	KURU	KURU
14	0.033	0.460	0.592	0.082	0.168	0.168	0.752	1.55	0.096	KURU	KURU	KURU
15	0.050	0.460	0.592	0.064	0.168	0.168	0.752	1.55	0.096	KURU	KURU	KURU
16	0.058	0.460	0.592	0.064	0.168	0.168	0.752	1.55	0.096	KURU	KURU	KURU
17	0.082	0.460	0.636	0.064	0.168	0.168	0.752	1.55	0.082	KURU	KURU	KURU
18	0.110	0.460	0.636	0.064	0.168	0.168	0.616	1.55	0.070	KURU	KURU	KURU
19	0.150	0.504	0.636	0.064	0.168	0.168	0.532	1.45	0.070	KURU	KURU	KURU
20	0.250	0.504	0.592	0.064	0.168	0.168	0.532	1.25	0.070	KURU	KURU	KURU
21	0.250	0.548	0.592	0.064	0.168	0.168	0.532	1.20	0.070	KURU	KURU	KURU
22	0.250	0.592	0.592	0.064	0.202	0.202	0.532	1.10	0.070	KURU	KURU	KURU
23	0.292	0.548	0.592	0.046	0.236	0.236	0.532	1.00	0.070	KURU	KURU	KURU
24	0.292	0.548	0.592	0.046	0.236	0.236	0.532	0.787	0.050	KURU	KURU	KURU
25	0.292	0.592	0.592	0.046	0.236	0.270	0.532	0.733	0.040	KURU	KURU	KURU
26	0.292	0.592	0.592	0.046	0.236	0.358	0.532	0.636	0.033	KURU	KURU	KURU
27	0.292	0.592	0.548	0.046	0.236	0.402	0.574	1.35	0.028	KURU	KURU	KURU
28	0.292	0.592	0.504	0.046	0.236	0.490	0.574	2.52	0.175	KURU	KURU	KURU
29	0.292	0.592	0.504	0.046	-----	0.658	0.574	1.65	0.225	KURU	KURU	KURU
30	0.292	0.592	0.548	0.046	-----	0.700	0.700	1.20	0.070	KURU	KURU	KURU
31	0.292	-----	0.548	0.046	-----	0.700	-----	0.893	-----	KURU	KURU	-----
Maks.	0.292	0.636	0.636	0.680	0.314	0.752	1.10	3.80	0.636	0.033	KURU	KURU
Min.	0.002	0.292	0.504	0.010	0.064	0.064	0.490	0.548	0.028	KURU	KURU	KURU
Ortalama	0.128	0.475	0.586	0.199	0.154	0.224	0.650	1.48	0.145	0.002	KURU	KURU
LT/SN/Km2	0.171	0.634	0.784	0.267	0.206	0.300	0.869	1.98	0.194	0.003	0.000	0.000
AKIM mm.	0.457	1.64	2.10	0.714	0.499	0.803	2.25	5.30	0.502	0.008	0.000	0.000
MİL. M3	0.342	1.23	1.57	0.534	0.373	0.601	1.69	3.96	0.376	0.006	0.000	0.000

SU YILI (2006) YILLIK TOPLAM AKIM 10.68 MİLYON M3 14 MM. 0.5 LT/SN/Km2

15. Kizilırmak Havzasi

D15A055 SARIKAYA DERESİ KADILI

YERİ : SORGUN SARIKAYA YOLUNUN 42.KM SİNDEKİ KADILI KÖYÜ İLKOKULU BAHÇESINDEDIR
35°17'50" Doğu - 39°32'26" Kuzey

YAĞIŞ ALANI : 362.80 km2 **YAKLAŞIK KOT :** 1058 m

GÖZLEM SÜRESİ : 15.10.1963 - 30.09.2006

ORTALAMA AKIMLAR : Gözlem süresinde 0.613 m3/sn. (41 Yıllık) 2006 Su yılında 0.201 m3/sn.

ANLIK EN ÇOK VE EN AZ AKIMLAR:

2006 Su yılında anlık ençok akım	:	0.991	m3/sn	30.04.2006
2006 Su yılında anlık enaz akım	:	0.000	m3/sn	01.10.2005
Gözlem süresinde anlık ençok akım	:	15.3	m3/sn	18.05.1990
Gözlem süresinde anlık enaz akım	:	0.000	m3/sn	14.06.1967

15. Anahtar Eğrisi (Seviyeler cm olarak)

Seviye	Akım	Seviye	Akım	Seviye	Akım	Seviye	Akım
1	0.000	6	0.045	24	0.920	66	3.5
2	0.000	9	0.153	35	1.3	73	4.4
3	0.001	12	0.286	38	1.5	76	4.8
4	0.003	14	0.400	46	1.9		
5	0.015	19	0.650	61	2.8		

Akımlar 01 Ekim 2005 'den 30 Eylül 2006' a kadar m3/sn olarak

Gün	Ekim	Kasım	Aralık	Ocak	Şubat	Mart	Nisan	Mayıs	Haziran	Temmuz	Ağustos	Eylül
01	0.002	0.139	0.180	0.180	0.543	0.275	0.454	0.454	0.139	0.098	0.057	KURU
02	0.002	0.139	0.180	0.180	0.454	0.364	0.454	0.454	0.139	0.098	0.057	KURU
03	0.002	0.139	0.180	0.275	0.454	0.364	0.454	0.543	0.139	0.098	0.057	KURU
04	0.002	0.139	0.180	0.275	0.454	0.364	0.454	0.454	0.139	0.057	0.057	KURU
05	0.002	0.139	0.180	0.275	0.543	0.364	0.454	0.454	0.139	0.057	0.057	KURU
06	0.013	0.139	0.180	0.275	0.454	0.364	0.454	0.364	0.139	0.057	0.057	KURU
07	0.035	0.139	0.180	0.275	0.454	0.454	0.454	0.364	0.057	0.057	0.057	KURU
08	0.057	0.139	0.180	0.275	0.454	0.454	0.454	0.364	0.057	0.057	0.057	0.002
09	0.057	0.139	0.180	0.275	0.364	0.454	0.364	0.364	0.057	0.057	0.057	0.013
10	0.057	0.139	0.180	0.364	0.364	0.454	0.364	0.364	0.057	0.057	0.057	0.013
11	0.057	0.139	0.180	0.364	0.275	0.454	0.364	0.275	0.057	0.057	0.057	0.013
12	0.057	0.139	0.180	0.454	0.275	0.454	0.275	0.275	0.057	0.057	0.057	0.013
13	0.057	0.139	0.180	0.454	0.275	0.454	0.275	0.275	0.057	0.057	0.057	0.013
14	0.057	0.139	0.180	0.543	0.275	0.454	0.364	0.275	0.098	0.057	0.057	0.013
15	0.057	0.139	0.180	0.543	0.275	0.454	0.364	0.275	0.098	0.057	0.057	0.013
16	0.057	0.139	0.180	0.543	0.275	0.454	0.364	0.275	0.098	0.057	0.035	0.013
17	0.057	0.139	0.180	0.543	0.275	0.454	0.364	0.275	0.098	0.057	0.002	0.013
18	0.057	0.139	0.180	0.543	0.275	0.454	0.364	0.275	0.098	0.057	KURU	0.013
19	0.057	0.139	0.180	0.454	0.180	0.454	0.364	0.275	0.098	0.057	KURU	0.013
20	0.057	0.139	0.180	0.454	0.180	0.454	0.364	0.180	0.098	0.057	KURU	0.013
21	0.057	0.139	0.180	0.454	0.180	0.454	0.364	0.180	0.098	0.057	KURU	0.013
22	0.057	0.139	0.180	0.543	0.275	0.454	0.364	0.180	0.098	0.057	KURU	0.035
23	0.057	0.180	0.180	0.543	0.275	0.454	0.275	0.139	0.098	0.057	KURU	0.035
24	0.098	0.180	0.180	0.543	0.275	0.454	0.180	0.139	0.098	0.057	KURU	0.057
25	0.098	0.180	0.180	0.543	0.275	0.454	0.275	0.139	0.098	0.057	KURU	0.057
26	0.139	0.180	0.180	0.543	0.180	0.454	0.275	0.098	0.098	0.057	KURU	0.057
27	0.139	0.180	0.180	0.543	0.180	0.454	0.275	0.139	0.098	0.057	KURU	0.098
28	0.139	0.180	0.180	0.543	0.180	0.454	0.275	0.139	0.098	0.057	KURU	0.098
29	0.139	0.180	0.180	0.633	-----	0.454	0.275	0.139	0.098	0.057	KURU	0.098
30	0.139	0.180	0.180	0.543	-----	0.454	0.275	0.139	0.098	0.057	KURU	0.098
31	0.139	-----	0.180	0.543	-----	0.454	-----	0.139	-----	0.057	KURU	-----
Maks.	0.139	0.180	0.180	0.633	0.633	0.633	0.991	0.633	0.364	0.139	0.098	0.098
Min.	KURU	0.139	0.180	0.139	0.139	0.275	0.139	0.098	KURU	0.057	KURU	KURU
Ortalama	0.065	0.150	0.180	0.436	0.319	0.434	0.355	0.271	0.097	0.061	0.029	0.027
LT/SN/Km2	0.178	0.413	0.496	1.20	0.878	1.20	0.979	0.747	0.266	0.168	0.079	0.074
AKIM mm.	0.476	1.07	1.33	3.22	2.12	3.20	2.54	2.00	0.690	0.450	0.212	0.191
MİL. M3	0.173	0.389	0.482	1.17	0.771	1.16	0.921	0.726	0.250	0.163	0.077	0.069

SU YILI (2006) YILLIK TOPLAM AKIM 6.35 MİLYON M3 18 MM. 0.6 LT/SN/Km2

15. Kizilirmak Havzasi

D15A056 EGRİÖZ DERESI SORGUN

YERİ : **YOZGAT-AKDAĞMADENİ YOLU 2 KM SONRA ESKİ KARA YOLUNA GİRİLİR500-600 METRE SONRA İSTASYONA VARILIR**
35°12'58" Doğu - 39°47'52" Kuzey

YAĞIŞ ALANI : **512,00 km2** **YAKLAŞIK KOT : 1058 m**

GÖZLEM SÜRESİ : **13.11.1963 - 30.09.2006**

ORTALAMA AKIMLAR : **Gözlem süresinde 1.508 m3/sn. (37 Yıllık) 2006 Su yılında 0.734 m3/sn.**

ANLIK EN ÇOK VE EN AZ AKIMLAR:

2006 Su yılında anlık ençok akım	**:**	**5.31**	**m3/sn**	**02.03.2006**
2006 Su yılında anlık enaz akım	**:**	**0.017**	**m3/sn**	**21.07.2006**
Gözlem süresinde anlık ençok akım	**:**	**92.0**	**m3/sn**	**22.01.1966**
Gözlem süresinde anlık enaz akım	**:**	**0.000**	**m3/sn**	**04.09.1984**

11. Anahtar Eğrisi (Seviyeler cm olarak)

Seviye	Akım	Seviye	Akım	Seviye	Akım	Seviye	Akım
5	0.000	15	0.031	45	1.8	120	10.6
7	0.002	17	0.052	55	2.8	140	13.2
9	0.005	19	0.081	65	3.8	160	15.8
11	0.009	25	0.270	80	5.6	180	18.4
13	0.017	35	1.0	100	8.1	200	21.0

Akımlar 01 Ekim 2005 'den 30 Eylül 2006' a kadar m3/sn olarak

Gün	Ekim	Kasım	Aralık	Ocak	Şubat	Mart	Nisan	Mayıs	Haziran	Temmuz	Ağustos	Eylül
01	0.100	0.100	0.202	0.202	0.336	4.08	2.80	1.58	0.236	0.065	0.031	0.031
02	0.100	0.100	0.202	0.236	0.336	4.36	3.10	1.85	0.236	0.065	0.031	0.040
03	0.100	0.100	0.202	0.270	0.336	3.70	3.10	1.85	0.202	0.065	0.031	0.040
04	0.100	0.134	0.236	0.270	0.336	5.31	2.60	1.76	0.168	0.065	0.031	0.040
05	0.081	0.134	0.270	0.270	0.336	3.50	2.50	1.67	0.134	0.065	0.024	0.040
06	0.081	0.134	0.236	0.270	0.402	3.00	2.30	1.67	0.134	0.065	0.024	0.031
07	0.081	0.134	0.236	0.236	0.468	2.70	2.21	1.58	0.134	0.065	0.024	0.040
08	0.100	0.134	0.236	0.270	0.680	2.60	2.12	1.40	0.134	0.065	0.024	0.031
09	0.100	0.134	0.236	0.270	0.840	2.70	2.03	1.24	0.134	0.040	0.024	0.031
10	0.100	0.134	0.236	0.270	0.840	2.40	2.03	1.24	0.134	0.040	0.024	0.031
11	0.100	0.134	0.236	0.270	1.00	2.21	2.03	1.24	0.100	0.040	0.024	0.031
12	0.100	0.134	0.236	0.270	3.70	2.12	1.85	1.24	0.202	0.040	0.024	0.031
13	0.100	0.134	0.236	0.270	3.80	1.94	1.76	1.00	0.236	0.040	0.024	0.031
14	0.100	0.134	0.236	0.270	2.70	1.67	1.76	0.760	0.336	0.031	0.024	0.031
15	0.100	0.134	0.236	0.270	2.21	1.94	1.76	0.760	0.336	0.031	0.024	0.031
16	0.134	0.134	0.236	0.236	1.85	1.94	2.12	0.760	0.336	0.024	0.024	0.031
17	0.100	0.134	0.236	0.202	1.76	1.85	1.94	0.840	0.336	0.024	0.024	0.031
18	0.100	0.134	0.236	0.236	1.67	1.94	1.85	0.760	0.236	0.024	0.024	0.031
19	0.100	0.134	0.236	0.468	1.76	2.12	1.76	0.760	0.236	0.024	0.024	0.031
20	0.100	0.134	0.236	0.402	2.30	2.60	1.76	0.680	0.202	0.024	0.024	0.031
21	0.100	0.134	0.236	0.270	2.40	3.40	1.67	0.680	0.168	0.017	0.024	0.031
22	0.100	0.168	0.236	0.336	2.50	3.80	1.67	0.680	0.134	0.024	0.024	0.031
23	0.100	0.168	0.236	0.336	2.60	3.60	1.67	0.600	0.081	0.040	0.024	0.052
24	0.100	0.168	0.236	0.336	2.90	3.20	1.67	0.534	0.065	0.040	0.024	0.024
25	0.100	0.202	0.236	0.336	3.50	3.20	1.67	0.468	0.065	0.040	0.024	0.052
26	0.100	0.202	0.236	0.336	4.22	3.94	1.67	0.468	0.065	0.040	0.024	0.100
27	0.100	0.202	0.202	0.336	4.62	4.08	1.67	0.468	0.065	0.040	0.024	0.065
28	0.100	0.202	0.168	0.336	3.80	3.50	1.58	0.468	0.065	0.031	0.024	0.065
29	0.100	0.202	0.168	0.336	-----	3.20	1.58	0.336	0.065	0.031	0.024	0.065
30	0.100	0.202	0.168	0.336	-----	2.90	1.58	0.270	0.081	0.031	0.024	0.065
31	0.100	-----	0.202	0.336	-----	2.80	-----	0.270	-----	0.031	0.024	-----
Maks.	0.134	0.202	0.270	0.760	5.19	5.31	3.50	2.40	1.16	0.065	0.031	0.100
Min.	0.081	0.100	0.134	0.100	0.336	1.58	1.58	0.236	0.065	0.017	0.024	0.017
Ortalama	0.099	0.148	0.225	0.293	1.94	2.98	1.99	0.964	0.169	0.041	0.025	0.041
LT/SN/Km2	0.194	0.288	0.440	0.573	3.78	5.82	3.89	1.88	0.329	0.080	0.049	0.079
AKIM mm.	0.519	0.747	1.18	1.53	9.15	15.6	10.1	5.04	0.853	0.214	0.130	0.205
MİL. M3	0.266	0.383	0.603	0.785	4.68	7.97	5.17	2.58	0.437	0.109	0.067	0.105

SU YILI (2006) YILLIK TOPLAM AKIM 23.16 MİLYON M3 45 MM. 1.4 LT/SN/Km2

15. Kizilirmak Havzasi

D15A066 Yozgat Ç. Y.Elmahacili

YERİ : 1986YOZGAT YERKÖY YOLUNUN 28.KM SİNDEN SOLA AYRILAN HAM YOLUN500.M SİNDEKİ YUKARI ELMAHACILI KÖYÜNDEDİR.
34°35'0" Doğu - 39°41'0" Kuzey

YAĞIŞ ALANI : 211,10 km2 **YAKLAŞIK KOT :** 929 m

GÖZLEM SÜRESİ : 11.09.1964 - 30.09.2006

ORTALAMA AKIMLAR : Gözlem süresinde 1.028 m3/sn. (41 Yıllık) 2006 Su yılında 0.590 m3/sn.

ANLIK EN ÇOK VE EN AZ AKIMLAR:

2006 Su yılında anlık ençok akım	:	2.04	m3/sn	16.04.2006
2006 Su yılında anlık enaz akım	:	0.003	m3/sn	14.08.2006
Gözlem süresinde anlık ençok akım	:	46.0	m3/sn	04.03.1967
Gözlem süresinde anlık enaz akım	:	0.000	m3/sn	16.06.1986

18. Anahtar Eğrisi (Seviyeler cm olarak)

Seviye	Akım	Seviye	Akım	Seviye	Akım	Seviye	Akım
1	0.000	16	0.650	71	8.2	131	21.1
4	0.009	19	0.960	91	11.5	141	23.5
7	0.068	26	1.8	101	13.9	151	25.9
10	0.200	41	3.8	111	16.3	161	28.3
13	0.400	56	6.0	121	18.7	171	30.7

Akımlar 01 Ekim 2005 'den 30 Eylül 2006' a kadar m3/sn olarak

Gün	Ekim	Kasım	Aralık	Ocak	Şubat	Mart	Nisan	Mayıs	Haziran	Temmuz	Ağustos	Eylül
01	0.145	0.400	0.760	0.760	0.760	1.41	1.41	1.05	0.200	0.260	0.021	0.003
02	0.200	0.400	0.650	0.760	0.760	1.28	1.41	0.860	0.200	0.260	0.021	0.009
03	0.260	0.480	0.650	0.760	0.760	1.41	1.41	0.760	0.145	0.200	0.021	0.003
04	0.260	0.560	0.560	0.650	0.760	1.41	1.28	0.860	0.145	0.145	0.009	0.003
05	0.260	1.28	0.650	0.650	0.560	1.41	1.28	0.860	0.100	0.145	0.009	0.009
06	0.260	1.15	0.650	0.960	0.560	1.28	1.28	0.860	0.100	0.145	0.009	0.009
07	0.260	0.860	0.650	0.960	0.960	1.28	1.28	0.860	0.100	0.145	0.009	0.021
08	0.260	0.650	0.650	0.860	0.860	1.28	1.28	0.760	0.100	0.145	0.009	0.021
09	0.260	0.560	0.650	0.860	1.05	1.28	1.28	0.760	0.100	0.100	0.009	0.021
10	0.260	0.560	0.650	0.760	1.15	1.28	1.28	0.760	0.100	0.100	0.009	0.021
11	0.260	0.480	0.650	0.760	1.15	1.15	1.15	0.760	0.100	0.068	0.009	0.021
12	0.260	0.400	0.650	0.760	1.41	1.15	1.15	0.760	0.400	0.068	0.009	0.021
13	0.330	0.400	0.650	0.760	1.80	1.15	1.15	0.760	0.330	0.068	0.009	0.021
14	0.330	0.480	0.560	0.760	1.54	1.15	1.05	0.650	0.260	0.068	0.009	0.021
15	0.330	0.480	0.560	0.760	1.15	1.15	1.41	0.560	0.260	0.068	0.003	0.021
16	0.400	0.400	0.650	0.760	1.15	1.05	1.80	0.560	0.330	0.068	0.003	0.021
17	0.860	0.480	0.650	0.560	1.15	1.05	1.15	0.560	0.260	0.040	0.003	0.021
18	0.960	0.480	0.650	0.560	1.28	1.05	1.05	0.560	0.260	0.040	0.003	0.021
19	0.760	0.960	0.650	0.480	1.28	1.15	0.960	0.480	0.260	0.040	0.003	0.021
20	0.650	1.05	0.760	0.480	1.28	1.28	0.860	0.480	0.260	0.040	0.003	0.021
21	0.560	1.41	0.560	0.560	1.41	1.28	0.760	0.480	0.260	0.040	0.009	0.021
22	0.560	1.28	0.560	0.560	1.54	1.15	0.760	0.480	0.200	0.040	0.009	0.021
23	0.560	1.15	0.560	0.650	1.41	1.67	0.760	0.400	0.200	0.040	0.009	0.040
24	0.560	1.15	0.560	0.650	1.28	1.92	0.760	0.400	0.145	0.040	0.003	0.040
25	0.560	1.05	0.560	0.650	1.15	1.92	0.650	0.260	0.100	0.040	0.003	0.100
26	0.480	0.960	0.650	0.760	1.15	1.92	0.650	0.200	0.100	0.040	0.003	0.760
27	0.480	0.760	0.650	0.760	1.54	1.92	0.650	0.145	0.100	0.021	0.003	0.480
28	0.480	0.760	0.650	0.650	1.54	1.80	0.650	0.200	0.100	0.021	0.003	0.400
29	0.480	0.760	0.650	0.760	-----	1.80	0.760	0.200	0.100	0.021	0.003	0.400
30	0.480	0.760	0.650	0.760	-----	1.67	1.41	0.200	0.200	0.021	0.003	0.650
31	0.480	-----	0.760	0.760	-----	1.67	-----	0.200	-----	0.021	0.003	-----
Maks.	0.960	1.54	0.760	1.05	1.92	1.92	2.04	1.15	0.480	0.260	0.021	1.05
Min.	0.145	0.400	0.560	0.480	0.560	0.960	0.650	0.145	0.100	0.021	0.003	0.003
Ortalama	0.427	0.752	0.637	0.714	1.16	1.40	1.09	0.570	0.184	0.083	0.007	0.108
LT/SN/Km2	2.02	3.56	3.02	3.38	5.48	6.63	5.17	2.70	0.871	0.391	0.035	0.512
AKIM mm.	5.42	9.23	8.09	9.06	13.3	17.8	13.4	7.24	2.26	1.05	0.095	1.33
MİL. M3	1.14	1.95	1.71	1.91	2.80	3.75	2.83	1.53	0.476	0.221	0.020	0.280

SU YILI (2006) YILLIK TOPLAM AKIM 18.62 MİLYON M3 88 MM. 2.8 LT/SN/Km2

15. Kizilirmak Havzasi

D15A069 MUSABEYLİ DERESİ MUSABEYLİ

YERİ : **YOZGAT - SUNGURLU YOLUNDAN MUSABEYLİ KÖYÜNE VARILIR.KİLLİKÖZÜ DERESİ ÜZERİNDEDİR**

34°38'29" Doğu - 39°50'51" Kuzey

YAĞIŞ ALANI : **143,10 km2** **YAKLAŞIK KOT : 952 m**

GÖZLEM SÜRESİ : **24.11.1986 - 30.09.2006**

ORTALAMA AKIMLAR : **Gözlem süresinde 0.665 m3/sn. (15 Yıllık) 2006 Su yılında 0.382 m3/sn.**

ANLIK EN ÇOK VE EN AZ AKIMLAR:

2006 Su yılında anlık ençok akım	**:**	**34.5**	**m3/sn**	**29.06.2006**
2006 Su yılında anlık enaz akım	**:**	**0.000**	**m3/sn**	**15.07.2006**
Gözlem süresinde anlık ençok akım	**:**	**60.5**	**m3/sn**	**21.06.1991**
Gözlem süresinde anlık enaz akım	**:**	**0.000**	**m3/sn**	**01.10.1986**

6. Anahtar Eğrisi (Seviyeler cm olarak)

Seviye	Akım	Seviye	Akım	Seviye	Akım	Seviye	Akım
1	0.000	20	0.654	41	4.6	90	29.2
3	0.000	24	1.0	45	5.4	100	34.5
5	0.001	28	1.6	49	6.8	120	46.4
7	0.016	32	2.3	55	9.4	140	56.0
13	0.173	36	3.3	60	11.3	160	66.0

Akımlar 01 Ekim 2005 'den 30 Eylül 2006' a kadar m3/sn olarak

Gün	Ekim	Kasım	Aralık	Ocak	Şubat	Mart	Nisan	Mayıs	Haziran	Temmuz	Ağustos	Eylül
01	0.005	0.036	0.141	0.109	0.077	2.58	1.47	0.654	0.057	0.282	KURU	KURU
02	0.005	0.057	0.141	0.109	0.077	2.82	1.47	0.741	0.057	0.227	KURU	KURU
03	0.036	0.077	0.141	0.109	1.16	3.84	1.47	0.741	0.036	0.173	KURU	KURU
04	0.016	0.109	0.109	0.109	0.227	2.82	1.31	0.741	0.036	0.173	KURU	KURU
05	0.016	0.109	0.109	0.141	0.109	2.16	1.16	0.654	0.036	0.109	KURU	KURU
06	0.005	0.077	0.109	0.141	0.141	1.98	1.00	0.575	0.036	0.109	KURU	KURU
07	0.005	0.057	0.109	0.141	0.173	1.98	1.00	0.575	0.016	0.077	KURU	KURU
08	0.005	0.057	0.109	0.141	0.336	1.98	1.00	0.575	0.016	0.077	KURU	KURU
09	0.005	0.057	0.077	0.109	0.416	1.98	1.00	0.575	0.016	0.057	KURU	KURU
10	0.001	0.057	0.077	0.109	0.336	1.62	0.914	0.495	0.016	0.036	KURU	KURU
11	0.001	0.057	0.077	0.109	0.654	1.47	0.914	0.495	0.057	0.005	KURU	KURU
12	0.001	0.057	0.077	0.141	1.00	1.31	0.914	0.495	0.077	0.001	KURU	KURU
13	0.005	0.057	0.077	0.141	0.914	1.16	0.914	0.495	0.057	0.001	KURU	KURU
14	0.005	0.077	0.077	0.141	0.741	1.31	0.827	0.495	0.036	0.001	KURU	KURU
15	0.005	0.077	0.109	0.141	0.654	1.31	0.914	0.416	0.036	KURU	KURU	KURU
16	0.016	0.057	0.141	0.077	0.575	1.16	0.914	0.416	0.016	KURU	KURU	KURU
17	0.036	0.057	0.141	0.057	0.416	1.16	0.827	0.416	0.016	KURU	KURU	KURU
18	0.036	0.077	0.141	0.057	0.575	1.00	0.827	0.336	0.016	KURU	KURU	KURU
19	0.036	0.077	0.109	0.173	0.827	1.16	0.741	0.336	0.036	KURU	KURU	KURU
20	0.016	0.173	0.109	0.173	1.47	1.62	0.741	0.282	0.036	KURU	KURU	KURU
21	0.016	0.336	0.109	0.141	1.31	1.98	0.654	0.227	0.036	KURU	KURU	KURU
22	0.016	0.575	0.109	0.141	1.98	2.58	0.654	0.173	0.036	KURU	KURU	KURU
23	0.016	0.495	0.109	0.077	1.62	2.82	0.654	0.141	0.016	KURU	KURU	KURU
24	0.016	0.336	0.109	0.057	1.62	2.34	0.654	0.109	0.016	KURU	KURU	KURU
25	0.016	0.282	0.109	0.057	1.98	2.34	0.654	0.077	0.016	KURU	KURU	KURU
26	0.016	0.173	0.077	0.057	1.80	2.34	0.575	0.077	0.005	KURU	KURU	0.057
27	0.036	0.141	0.077	0.057	1.98	1.98	0.575	0.057	0.016	KURU	KURU	0.057
28	0.036	0.141	0.077	0.057	1.98	1.98	0.575	0.057	0.036	KURU	KURU	0.057
29	0.036	0.141	0.077	0.077	-----	1.80	0.575	0.057	2.16	KURU	KURU	0.057
30	0.036	0.141	0.077	0.077	-----	1.62	0.654	0.057	0.495	KURU	KURU	0.077
31	0.036	-----	0.077	0.057	-----	1.62	-----	0.057	-----	KURU	KURU	-----
Maks.	0.036	0.654	0.141	0.173	2.34	4.10	1.47	0.741	34.5	0.282	KURU	0.077
Min.	0.001	0.036	0.077	0.036	0.077	1.00	0.575	0.057	0.005	KURU	KURU	KURU
Ortalama	0.017	0.141	0.103	0.106	0.898	1.93	0.885	0.374	0.118	0.043	KURU	0.010
LT/SN/Km2	0.120	0.983	0.718	0.740	6.28	13.5	6.18	2.61	0.824	0.299	0.000	0.071
AKIM mm.	0.321	2.55	1.92	1.98	15.2	36.1	16.0	7.00	2.14	0.802	0.000	0.184
MİL. M3	0.046	0.365	0.275	0.284	2.17	5.17	2.29	1.00	0.306	0.115	0.000	0.026

SU YILI (2006) YILLIK TOPLAM AKIM 12.05 MİLYON M3 84 MM. 2.7 LT/SN/Km2

15. Kizilirmak Havzasi

D15A070 INANDİK DERESİ ARİFEOGLU

YERİ : **YOZGAT ANKARA KARAYOLUNUN 25.KM SİNDEN ARİFOĞLU KÖYÜNEGİRİLİR.KÖYÜN 200 METRE BATISINDADIR**

34°19'34" Doğu - 39°43'46" Kuzey

YAĞIŞ ALANI : **367,40 km2** **YAKLAŞIK KOT : 739 m**

GÖZLEM SÜRESİ : **17.09.1964 - 30.09.2006**

ORTALAMA AKIMLAR : **Gözlem süresinde 0.679 m3/sn. (14 Yıllık) 2006 Su yılında 0.729 m3/sn.**

ANLIK EN ÇOK VE EN AZ AKIMLAR:

2006 Su yılında anlık ençok akım	**:**	**13.8**	**m3/sn**	**20.11.2005**
2006 Su yılında anlık enaz akım	**:**	**0.000**	**m3/sn**	**30.11.2005**
Gözlem süresinde anlık ençok akım	**:**	**31.3**	**m3/sn**	**20.08.2005**
Gözlem süresinde anlık enaz akım	**:**	**0.000**	**m3/sn**	**29.07.1987**

3. Anahtar Eğrisi (Seviyeler cm olarak)

Seviye	Akım	Seviye	Akım	Seviye	Akım	Seviye	Akım
1	0.000	8	0.082	21	2.3	61	15.3
3	0.001	9	0.140	26	3.7	71	19.5
5	0.012	10	0.200	31	5.1	81	23.7
6	0.025	11	0.320	41	8.2	91	27.9
7	0.048	16	1.1	51	11.2	101	32.2

Akımlar 01 Ekim 2005 'den 30 Eylül 2006' a kadar m3/sn olarak

Gün	Ekim	Kasım	Aralık	Ocak	Şubat	Mart	Nisan	Mayıs	Haziran	Temmuz	Ağustos	Eylül
01	0.420	0.105	KURU	0.047	0.105	3.40	0.632	1.10	0.005	0.660	0.800	0.476
02	0.420	0.198	KURU	0.047	0.105	4.32	0.632	1.58	0.005	0.660	0.800	0.476
03	0.420	0.297	KURU	0.047	0.105	5.90	0.632	1.34	0.005	0.297	0.800	0.632
04	0.420	0.297	0.660	0.047	0.105	5.90	0.632	0.944	KURU	0.420	0.420	0.632
05	0.420	0.297	2.55	0.047	0.105	3.40	0.632	0.944	KURU	0.198	0.420	0.632
06	0.420	0.198	2.55	0.047	0.105	3.12	0.476	0.944	0.105	0.105	0.800	0.320
07	0.800	0.105	2.55	0.047	0.105	2.83	0.476	0.944	0.198	0.047	0.660	0.476
08	0.800	0.105	2.55	0.047	0.198	2.83	0.320	1.10	0.800	0.047	0.660	0.082
09	0.198	0.105	2.55	0.047	0.297	2.27	0.200	1.10	1.03	0.047	0.420	0.082
10	0.105	0.105	2.55	0.047	0.198	1.70	0.320	1.10	1.25	0.047	0.476	0.140
11	0.047	0.105	2.27	0.047	0.420	1.70	0.632	0.788	1.25	0.105	0.476	0.320
12	0.105	0.105	2.27	0.047	2.55	1.48	0.632	0.788	1.25	0.019	0.632	0.476
13	0.105	0.198	2.27	0.047	1.70	1.48	0.320	0.944	0.660	0.047	0.476	0.476
14	0.105	0.297	2.55	0.047	1.03	1.98	0.320	0.944	0.420	0.047	0.476	0.632
15	0.105	0.297	3.12	0.047	1.25	2.27	0.476	0.944	0.420	0.105	0.476	0.632
16	0.047	0.198	3.12	0.047	0.660	1.98	0.200	0.944	0.660	0.420	0.476	0.632
17	0.047	0.198	2.83	0.047	0.297	1.98	0.140	0.944	0.660	0.420	0.200	0.476
18	0.047	0.297	2.83	0.047	0.297	1.70	0.476	0.944	0.420	0.420	0.200	0.320
19	0.047	0.660	1.03	0.047	0.660	1.98	0.476	0.788	0.660	0.420	0.200	0.476
20	0.047	6.55	0.047	0.105	1.03	2.83	0.140	0.632	0.420	0.198	0.200	0.476
21	0.047	4.01	0.047	0.105	1.25	4.01	0.200	0.476	0.660	0.198	0.788	0.476
22	0.019	1.03	0.019	0.105	1.98	5.58	0.320	0.476	0.660	0.297	0.476	0.200
23	0.019	0.660	0.019	0.105	2.55	4.01	0.320	0.320	0.420	0.660	0.632	0.200
24	0.019	0.420	0.019	0.105	2.83	2.06	0.320	0.320	0.420	0.660	0.320	0.788
25	0.105	0.297	0.047	0.105	3.71	1.34	0.320	0.320	0.198	0.660	0.320	0.476
26	0.297	0.198	0.047	0.105	4.32	1.10	0.632	0.047	0.105	0.800	0.476	KURU
27	0.297	0.198	0.047	0.105	3.12	0.944	0.632	0.005	0.019	1.03	0.320	0.320
28	0.297	0.198	0.019	0.105	3.12	0.788	0.476	0.005	0.198	0.800	0.632	0.200
29	0.198	0.105	0.019	0.105	-----	0.788	0.788	0.005	0.420	0.660	0.632	0.200
30	0.198	0.019	0.047	0.105	-----	0.632	0.944	0.005	0.660	0.660	0.944	0.140
31	0.105	-----	0.047	0.105	-----	0.632	-----	0.005	-----	0.660	0.788	-----
Maks.	1.03	13.8	3.12	0.198	8.17	9.60	4.54	3.14	1.98	1.98	4.26	0.788
Min.	0.019	KURU	KURU	0.019	0.001	0.105	0.012	0.005	KURU	0.019	0.105	KURU
Ortalama	0.217	0.595	1.25	0.069	1.22	2.48	0.457	0.701	0.466	0.381	0.529	0.395
LT/SN/Km2	0.591	1.62	3.40	0.189	3.32	6.75	1.24	1.91	1.27	1.04	1.44	1.08
AKIM mm.	1.58	4.20	9.09	0.506	8.04	18.1	3.23	5.11	3.29	2.78	3.86	2.79
MİL. M3	0.581	1.54	3.34	0.186	2.96	6.65	1.19	1.88	1.21	1.02	1.42	1.03

SU YILI (2006) YILLIK TOPLAM AKIM 23.01 MİLYON M3 63 MM. 2.0 LT/SN/Km2

15. Kizilirmak Havzasi

D15A074 KAMERÖZÜ SUYU GÜNDÜZLÜ

YERİ : **SARIKAYA İLÇESİNE 25 KM MESAFEDEKİ HASBEK BUCAĞI ARAPTAŞIKÖY YOLUNUN 6.5 KM.SİNDEKİ KÖPRÜDEDİR.**
35°34'49" Doğu - 39°31'4" Kuzey

YAĞIŞ ALANI : **91,70 km2** **YAKLAŞIK KOT : 1142 m**

GÖZLEM SÜRESİ : **01.10.1964 - 30.09.2006**

ORTALAMA AKIMLAR : **Gözlem süresinde 0.310 m3/sn. (41 Yıllık) 2006 Su yılında 0.104 m3/sn.**

ANLIK EN ÇOK VE EN AZ AKIMLAR:

2006 Su yılında anlık ençok akım	:	**0.280**	**m3/sn**	**02.04.2006**
2006 Su yılında anlık enaz akım	:	**0.003**	**m3/sn**	**17.07.2006**
Gözlem süresinde anlık ençok akım	:	**16.5**	**m3/sn**	**28.05.1968**
Gözlem süresinde anlık enaz akım	:	**0.000**	**m3/sn**	**07.08.1965**

10. Anahtar Eğrisi (Seviyeler cm olarak)

Seviye	Akım	Seviye	Akım	Seviye	Akım	Seviye	Akım
1	0.003	12	0.335	30	1.7	90	6.8
3	0.023	14	0.460	40	2.6	100	7.7
5	0.067	16	0.595	50	3.4	110	8.6
7	0.127	18	0.720	70	5.2	120	9.4
10	0.225	20	0.870	80	6.0	130	10.3

Akımlar 01 Ekim 2005 'den 30 Eylül 2006' a kadar m3/sn olarak

Gün	Ekim	Kasım	Aralık	Ocak	Şubat	Mart	Nisan	Mayıs	Haziran	Temmuz	Ağustos	Eylül
01	0.042	0.067	0.127	0.127	0.127	0.225	0.180	0.225	0.154	0.023	0.003	0.003
02	0.042	0.067	0.127	0.127	0.127	0.225	0.225	0.225	0.154	0.023	0.003	0.003
03	0.042	0.067	0.127	0.127	0.127	0.225	0.280	0.225	0.127	0.023	0.003	0.003
04	0.042	0.067	0.127	0.127	0.127	0.225	0.225	0.225	0.127	0.023	0.003	0.003
05	0.042	0.067	0.127	0.127	0.127	0.225	0.225	0.225	0.127	0.023	0.003	0.003
06	0.042	0.067	0.127	0.127	0.127	0.225	0.225	0.180	0.096	0.023	0.003	0.003
07	0.042	0.096	0.127	0.127	0.127	0.225	0.225	0.225	0.096	0.023	0.003	0.003
08	0.042	0.096	0.127	0.127	0.154	0.225	0.225	0.225	0.096	0.023	0.003	0.003
09	0.042	0.096	0.127	0.127	0.154	0.225	0.225	0.225	0.067	0.008	0.003	0.003
10	0.042	0.096	0.127	0.127	0.154	0.225	0.225	0.225	0.067	0.008	0.003	0.003
11	0.042	0.096	0.127	0.127	0.154	0.225	0.225	0.225	0.067	0.008	0.003	0.003
12	0.042	0.096	0.127	0.127	0.154	0.225	0.180	0.225	0.067	0.008	0.003	0.003
13	0.042	0.096	0.127	0.127	0.154	0.225	0.180	0.225	0.067	0.008	0.003	0.003
14	0.042	0.096	0.127	0.127	0.154	0.180	0.180	0.225	0.067	0.008	0.003	0.003
15	0.042	0.096	0.127	0.127	0.154	0.154	0.180	0.180	0.067	0.008	0.003	0.003
16	0.067	0.096	0.127	0.127	0.154	0.180	0.180	0.225	0.067	0.008	0.003	0.003
17	0.067	0.096	0.127	0.127	0.154	0.225	0.180	0.225	0.067	0.008	0.003	0.003
18	0.067	0.096	0.127	0.127	0.154	0.180	0.180	0.225	0.042	0.008	0.003	0.003
19	0.067	0.096	0.127	0.127	0.154	0.180	0.180	0.225	0.042	0.008	0.003	0.003
20	0.067	0.096	0.127	0.127	0.154	0.180	0.180	0.225	0.042	0.008	0.003	0.003
21	0.067	0.127	0.127	0.127	0.154	0.154	0.180	0.180	0.042	0.008	0.003	0.003
22	0.067	0.127	0.127	0.127	0.154	0.154	0.180	0.180	0.042	0.008	0.003	0.003
23	0.067	0.127	0.127	0.154	0.154	0.154	0.180	0.154	0.042	0.008	0.003	0.003
24	0.067	0.127	0.127	0.154	0.180	0.154	0.225	0.154	0.042	0.008	0.003	0.003
25	0.067	0.127	0.127	0.154	0.180	0.154	0.225	0.127	0.023	0.003	0.003	0.003
26	0.067	0.127	0.127	0.154	0.180	0.180	0.225	0.127	0.023	0.003	0.003	0.003
27	0.067	0.127	0.127	0.154	0.225	0.225	0.225	0.127	0.042	0.003	0.003	0.003
28	0.067	0.127	0.127	0.154	0.225	0.180	0.225	0.180	0.023	0.003	0.003	0.003
29	0.067	0.127	0.127	0.154	-----	0.180	0.225	0.154	0.023	0.003	0.003	0.003
30	0.067	0.127	0.127	0.127	-----	0.180	0.225	0.154	0.023	0.003	0.003	0.003
31	0.067	-----	0.127	0.127	-----	0.180	-----	0.154	-----	0.003	0.003	-----
Maks.	0.067	0.127	0.154	0.154	0.225	0.225	0.280	0.280	0.154	0.023	0.003	0.003
Min.	0.042	0.067	0.096	0.096	0.096	0.154	0.180	0.127	0.023	0.003	0.003	0.003
Ortalama	0.055	0.101	0.127	0.133	0.155	0.197	0.207	0.197	0.068	0.011	0.003	0.003
LT/SN/Km2	0.599	1.10	1.38	1.45	1.69	2.15	2.26	2.15	0.738	0.117	0.033	0.033
AKIM mm.	1.60	2.84	3.71	3.89	4.09	5.75	5.86	5.75	1.91	0.314	0.088	0.085
MİL. M3	0.147	0.261	0.340	0.356	0.375	0.527	0.537	0.527	0.175	0.029	0.008	0.008

SU YILI (2006) YILLIK TOPLAM AKIM 3.29 MİLYON M3 36 MM. 1.1 LT/SN/Km2

15. Kizilirmak Havzasi

D15A078 BAŞVEREN Ç. TERZİLİ

YERİ : **KASTAMONU-AKKAYA YOLUNUN 23.KM SİNDEN SOLA AYRILAN HATİPOĞLU-KİRENLI YOLLARININ 5.KM SİNDE TERZİLİ KÖYÜNDEDİR. 34°4'9" Doğu - 41°19'1" Kuzey**

YAĞIŞ ALANI : **440,60 km2** **YAKLAŞIK KOT : 953 m**

GÖZLEM SÜRESİ : **20.06.1964 - 30.09.2006**

ORTALAMA AKIMLAR : **Gözlem süresinde 2.962 m3/sn. (28 Yıllık) 2006 Su yılında 1.470 m3/sn.**

ANLIK EN ÇOK VE EN AZ AKIMLAR:

2006 Su yılında anlık ençok akım	:	**9.40**	**m3/sn**	**24.03.2006**
2006 Su yılında anlık enaz akım	:	**0.400**	**m3/sn**	**17.08.2006**
Gözlem süresinde anlık ençok akım	:	**105.**	**m3/sn**	**12.03.1968**
Gözlem süresinde anlık enaz akım	:	**0.005**	**m3/sn**	**12.09.2002**

2011. Anahtar Eğrisi (Seviyeler cm olarak)

Seviye	Akım	Seviye	Akım	Seviye	Akım	Seviye	Akım
3	0.019	87	10.7	172	87.3	258	359.
19	0.271	104	17.9	190	121.	276	463.
36	1.0	121	28.4	206	161.	295	596.
53	2.7	138	42.9	223	214.	315	767.
70	5.7	155	62.0	241	279.	337	988.

Akımlar 01 Ekim 2005 'den 30 Eylül 2006' a kadar m3/sn olarak

Gün	Ekim	Kasım	Aralık	Ocak	Şubat	Mart	Nisan	Mayıs	Haziran	Temmuz	Ağustos	Eylül
01	0.750	0.825	1.43	1.13	0.900	2.95	5.60	2.00	1.20	0.975	0.550	0.400
02	0.700	0.825	1.28	1.13	0.825	3.10	5.60	2.00	1.20	0.900	0.550	0.700
03	1.05	0.750	1.28	1.13	0.825	3.40	5.00	1.90	1.20	0.900	0.500	0.600
04	0.825	0.750	1.20	1.13	0.825	2.95	4.60	1.70	1.28	0.900	0.500	0.550
05	0.750	0.825	1.20	1.13	0.825	2.80	4.40	1.70	1.13	0.825	0.500	0.500
06	0.700	0.825	1.13	1.13	0.825	3.10	4.20	1.70	1.20	0.825	0.500	0.500
07	0.700	0.900	1.05	1.20	0.900	3.55	4.40	2.30	1.20	0.825	0.450	0.500
08	0.700	0.900	1.05	1.13	0.825	4.60	5.20	3.25	1.43	0.825	0.450	0.500
09	0.700	0.900	0.975	1.05	0.900	4.40	5.00	2.80	1.50	0.825	0.450	0.450
10	0.650	0.825	0.975	1.05	0.825	3.70	4.80	2.65	1.70	0.750	0.450	0.450
11	0.650	0.825	0.975	1.05	0.900	3.25	4.60	2.40	2.10	0.700	0.450	0.450
12	0.650	0.825	0.975	1.05	0.975	3.25	4.40	2.20	1.80	0.700	0.450	0.450
13	0.650	0.750	0.825	1.05	0.900	3.70	4.20	2.40	1.43	0.650	0.450	0.500
14	0.650	0.750	0.825	0.975	0.975	4.80	3.85	2.30	2.30	0.650	0.450	0.500
15	0.650	0.825	0.825	0.975	0.975	4.40	3.85	2.10	1.90	0.650	0.450	0.450
16	0.700	0.825	0.825	0.900	1.13	3.85	3.40	2.00	1.70	0.650	0.450	0.450
17	0.750	0.825	0.825	0.900	1.28	3.55	3.10	2.00	1.50	0.700	0.400	0.450
18	0.700	0.825	0.825	0.900	1.05	3.25	2.80	1.90	1.35	0.700	0.400	0.450
19	0.700	0.825	1.05	0.825	1.05	3.10	2.65	1.90	1.20	0.650	0.400	0.450
20	0.750	0.900	1.13	0.825	1.13	2.95	2.50	1.90	1.20	0.650	0.400	0.450
21	0.750	2.10	1.13	0.825	1.20	2.95	2.65	1.70	1.13	0.650	0.400	0.550
22	0.700	1.43	1.13	0.825	1.35	3.10	2.40	1.60	1.13	0.650	0.400	0.550
23	0.700	1.20	1.13	0.825	1.43	5.00	2.30	1.70	1.05	0.900	0.400	0.550
24	0.700	1.20	1.13	0.825	1.60	7.20	2.20	1.50	1.05	1.13	0.450	0.600
25	0.700	1.28	1.13	0.825	1.90	6.40	2.10	1.50	0.975	0.825	0.450	0.900
26	0.700	1.60	1.05	0.825	2.65	5.20	2.00	1.43	0.975	0.700	0.400	0.825
27	0.700	1.90	1.05	0.825	2.80	4.60	2.00	1.50	0.975	0.650	0.400	0.650
28	0.700	1.90	0.975	0.900	2.65	4.60	2.00	1.43	0.975	0.650	0.400	0.600
29	0.700	1.70	1.05	0.900	-----	4.60	1.90	1.35	0.900	0.650	0.400	0.600
30	0.750	1.60	1.05	1.13	-----	5.60	1.90	1.35	0.975	0.600	0.400	0.650
31	0.750	-----	1.05	1.13	-----	6.60	-----	1.28	-----	0.600	0.400	-----
Maks.	1.70	2.80	1.50	1.28	3.25	9.40	6.40	3.70	3.55	2.80	0.600	1.13
Min.	0.650	0.750	0.825	0.825	0.700	2.50	1.90	1.20	0.500	0.600	0.400	0.400
Ortalama	0.717	1.08	1.05	0.984	1.23	4.08	3.52	1.92	1.32	0.750	0.442	0.541
LT/SN/Km2	1.63	2.45	2.38	2.23	2.79	9.26	7.99	4.35	3.00	1.70	1.00	1.23
AKIM mm.	4.36	6.36	6.38	5.98	6.75	24.8	20.7	11.7	7.78	4.56	2.69	3.18
MİL. M3	1.92	2.80	2.81	2.63	2.97	10.9	9.12	5.14	3.43	2.01	1.18	1.40

SU YILI (2006) YILLIK TOPLAM AKIM 46.31 MİLYON M3 105 MM. 3.3 LT/SN/Km2

15. Kizilirmak Havzasi

D15A091 KARAMUK D. BUDAKLAR

YERİ : **KASTAMONU İLİ, DADAY İLÇESİ AŞAĞIKARAMIK KÖYÜ YOLUNUN 8.KM SINDEKİ KAYABAĞI VE BUDAKLI KÖYLERİ ARASINDADIR.**
33°29'41" Doğu - 41°29'40" Kuzey

YAĞIŞ ALANI : **49,30 km2** **YAKLAŞIK KOT : 869 m**

GÖZLEM SÜRESİ : **09.07.1965 - 30.09.2006**

ORTALAMA AKIMLAR : **Gözlem süresinde 0.187 m3/sn. (35 Yıllık) 2006 Su yılında 0.096 m3/sn.**

ANLIK EN ÇOK VE EN AZ AKIMLAR:

2006 Su yılında anlık ençok akım	:	**1.82**	**m3/sn**	**03.03.2006**
2006 Su yılında anlık enaz akım	:	**0.000**	**m3/sn**	**01.10.2005**
Gözlem süresinde anlık ençok akım	:	**64.0**	**m3/sn**	**04.07.1972**
Gözlem süresinde anlık enaz akım	:	**0.000**	**m3/sn**	**09.10.1965**

Akımlar 01 Ekim 2005 'den 30 Eylül 2006' a kadar m3/sn olarak

Gün	Ekim	Kasım	Aralık	Ocak	Şubat	Mart	Nisan	Mayıs	Haziran	Temmuz	Ağustos	Eylül
01	KURU	KURU	0.019	0.100	0.019	0.970	0.250	0.100	0.010	KURU	KURU	KURU
02	KURU	KURU	0.019	0.100	0.019	0.880	0.250	0.100	0.010	KURU	KURU	KURU
03	KURU	KURU	0.019	0.100	0.019	1.26	0.250	0.100	0.019	KURU	KURU	KURU
04	KURU	KURU	0.019	0.100	0.019	0.790	0.250	0.100	0.019	KURU	KURU	KURU
05	KURU	KURU	0.019	0.100	0.019	0.624	0.250	0.100	0.010	KURU	KURU	KURU
06	KURU	KURU	0.019	0.050	0.019	0.548	0.250	0.100	0.010	KURU	KURU	KURU
07	KURU	KURU	0.019	0.050	0.019	0.548	0.200	0.100	0.010	KURU	KURU	KURU
08	KURU	KURU	0.019	0.050	0.019	0.700	0.200	0.130	0.019	KURU	KURU	KURU
09	KURU	KURU	0.019	0.050	0.019	0.548	0.200	0.200	0.100	KURU	KURU	KURU
10	KURU	KURU	0.019	0.050	0.019	0.548	0.130	0.200	0.130	KURU	KURU	KURU
11	KURU	KURU	0.019	0.050	0.019	0.548	0.130	0.130	0.100	KURU	KURU	KURU
12	KURU	KURU	0.019	0.050	0.100	0.790	0.130	0.130	0.130	KURU	KURU	KURU
13	KURU	KURU	0.019	0.050	0.050	0.880	0.130	0.200	0.100	KURU	KURU	KURU
14	KURU	KURU	0.019	0.050	0.050	0.700	0.100	0.250	0.100	KURU	KURU	KURU
15	KURU	KURU	0.019	0.050	0.050	0.624	0.100	0.200	0.100	KURU	KURU	KURU
16	KURU	KURU	0.019	0.019	0.050	0.472	0.100	0.200	0.100	KURU	KURU	KURU
17	KURU	KURU	0.019	0.050	0.050	0.472	0.050	0.200	0.050	KURU	KURU	KURU
18	KURU	KURU	0.019	0.050	0.100	0.396	0.100	0.200	0.019	KURU	KURU	KURU
19	KURU	KURU	0.019	0.050	0.320	0.396	0.100	0.130	0.010	KURU	KURU	KURU
20	KURU	KURU	0.019	0.050	0.396	0.396	0.100	0.130	0.010	KURU	KURU	KURU
21	KURU	KURU	0.010	0.019	0.548	0.396	0.100	0.130	0.010	KURU	KURU	KURU
22	KURU	KURU	0.010	0.019	0.548	0.320	0.100	0.100	0.019	KURU	KURU	KURU
23	KURU	KURU	0.010	0.019	0.548	0.396	0.100	0.100	0.010	KURU	KURU	KURU
24	KURU	KURU	0.019	0.019	0.472	0.396	0.100	0.100	0.010	KURU	KURU	KURU
25	KURU	KURU	0.050	0.019	0.880	0.320	0.050	0.050	0.010	KURU	KURU	KURU
26	KURU	KURU	0.050	0.019	1.06	0.250	0.100	0.050	0.010	KURU	KURU	KURU
27	KURU	KURU	0.050	0.019	0.970	0.250	0.100	0.050	0.010	KURU	KURU	KURU
28	KURU	KURU	0.050	0.019	0.970	0.250	0.100	0.050	0.010	KURU	KURU	KURU
29	KURU	KURU	0.050	0.019	-----	0.250	0.100	0.050	0.010	KURU	KURU	KURU
30	KURU	KURU	0.050	0.019	-----	0.250	0.100	0.019	0.010	KURU	KURU	KURU
31	KURU	-----	0.100	0.019	-----	0.250	-----	0.010	-----	KURU	KURU	-----
Maks.	KURU	KURU	0.100	0.100	1.15	1.82	0.250	0.320	0.250	KURU	KURU	KURU
Min.	KURU	KURU	0.010	0.019	0.006	0.250	0.050	0.010	0.010	KURU	KURU	KURU
Ortalama	KURU	KURU	0.027	0.046	0.263	0.530	0.141	0.120	0.039	KURU	KURU	KURU
LT/SN/Km2	0.000	0.000	0.542	0.934	5.34	10.7	2.85	2.43	0.788	0.000	0.000	0.000
AKIM mm.	0.000	0.000	1.45	2.50	12.9	28.8	7.40	6.50	2.04	0.000	0.000	0.000
MİL. M3	0.000	0.000	0.072	0.123	0.637	1.42	0.365	0.320	0.101	0.000	0.000	0.000

SU YILI (2006) YILLIK TOPLAM AKIM 3.04 MİLYON M3 62 MM. 2.0 LT/SN/Km2

15. Kizilirmak Havzasi

D15A092 ESE D. VAKFIBELVEREN

YERİ : **KASTAMONU İLİ, TAŞKÖPRÜ İLÇESİ VAKFIBELVEREN KÖYÜNÜN 600.M MANSABINDADIR.**
34°16'31" Doğu - 41°29'37" Kuzey

YAĞIŞ ALANI : **313,20 km2** **YAKLAŞIK KOT : 665 m**

GÖZLEM SÜRESİ : **21.07.1965 - 30.09.2006**

ORTALAMA AKIMLAR : **Gözlem süresinde 0.856 m3/sn. (34 Yıllık) 2006 Su yılında 0.239 m3/sn.**

ANLIK EN ÇOK VE EN AZ AKIMLAR:

2006 Su yılında anlık ençok akım	**:**	**3.90**	**m3/sn**	**03.03.2006**
2006 Su yılında anlık enaz akım	**:**	**0.003**	**m3/sn**	**22.08.2006**
Gözlem süresinde anlık ençok akım	**:**	**200.**	**m3/sn**	**12.04.1966**
Gözlem süresinde anlık enaz akım	**:**	**0.000**	**m3/sn**	**01.10.1973**

10. Anahtar Eğrisi (Seviyeler cm olarak)

Seviye	Akım	Seviye	Akım	Seviye	Akım	Seviye	Akım
11	0.001	55	1.2	100	7.0	150	19.5
18	0.006	65	2.0	110	8.8	200	32.0
25	0.030	75	3.0	120	11.0	220	37.0
35	0.200	85	3.9	130	14.0	250	45.0
45	0.580	95	5.8	140	16.5	275	52.0

Akımlar 01 Ekim 2005 'den 30 Eylül 2006' a kadar m3/sn olarak

Gün	Ekim	Kasım	Aralık	Ocak	Şubat	Mart	Nisan	Mayıs	Haziran	Temmuz	Ağustos	Eylül
01	0.013	0.040	0.200	0.176	0.176	0.232	0.492	0.152	0.080	0.060	0.040	0.003
02	0.013	0.040	0.200	0.176	0.176	2.39	0.492	0.152	0.080	0.060	0.040	0.003
03	0.013	0.060	0.200	0.176	0.152	2.70	0.448	0.152	0.060	0.080	0.040	0.003
04	0.013	0.060	0.200	0.176	0.128	2.39	0.404	0.128	0.060	0.060	0.040	0.003
05	0.013	0.080	0.200	0.200	0.128	1.74	0.404	0.128	0.060	0.060	0.080	0.005
06	0.013	0.104	0.176	0.200	0.128	1.44	0.360	0.128	0.060	0.040	0.104	0.005
07	0.013	0.104	0.152	0.200	0.152	1.36	0.360	0.152	0.060	0.040	0.104	0.005
08	0.013	0.080	0.152	0.200	0.152	1.36	0.328	0.580	0.080	0.040	0.080	0.005
09	0.013	0.080	0.152	0.200	0.176	1.67	0.328	0.580	0.128	0.040	0.040	0.005
10	0.013	0.080	0.152	0.200	0.200	1.67	0.296	0.404	0.264	0.040	0.040	0.005
11	0.020	0.080	0.176	0.200	0.200	1.60	0.296	0.360	0.200	0.040	0.040	0.013
12	0.020	0.080	0.176	0.176	0.232	1.67	0.296	0.328	0.296	0.040	0.040	0.013
13	0.020	0.104	0.176	0.176	0.232	1.74	0.296	0.448	0.200	0.040	0.040	0.013
14	0.020	0.104	0.200	0.176	0.232	1.74	0.264	0.736	0.232	0.040	0.040	0.013
15	0.020	0.104	0.200	0.176	0.232	1.60	0.264	0.580	0.232	0.040	0.040	0.013
16	0.020	0.104	0.200	0.176	0.232	1.52	0.232	0.448	0.200	0.040	0.040	0.020
17	0.020	0.080	0.152	0.176	0.232	1.44	0.200	0.404	0.176	0.040	0.040	0.020
18	0.020	0.080	0.176	0.176	0.232	1.36	0.176	0.328	0.128	0.040	0.040	0.020
19	0.020	0.080	0.200	0.176	0.232	1.36	0.176	0.296	0.104	0.040	0.040	0.020
20	0.020	0.104	0.232	0.176	0.232	1.36	0.176	0.296	0.104	0.040	0.040	0.013
21	0.020	0.128	0.264	0.176	0.232	1.28	0.176	0.264	0.060	0.040	0.040	0.005
22	0.030	0.152	0.200	0.176	0.232	1.20	0.264	0.232	0.060	0.040	0.013	0.005
23	0.030	0.152	0.200	0.200	0.232	1.20	0.200	0.200	0.060	0.040	0.003	0.005
24	0.030	0.152	0.200	0.200	0.232	1.20	0.200	0.176	0.060	0.040	0.003	0.013
25	0.030	0.152	0.200	0.200	0.232	1.28	0.176	0.152	0.060	0.040	0.003	0.013
26	0.040	0.152	0.200	0.200	0.232	1.28	0.176	0.152	0.060	0.040	0.003	0.005
27	0.040	0.152	0.232	0.200	0.232	1.06	0.176	0.152	0.060	0.040	0.003	0.005
28	0.040	0.176	0.232	0.152	0.232	0.632	0.152	0.152	0.060	0.040	0.003	0.005
29	0.040	0.176	0.176	0.152	-----	0.536	0.128	0.128	0.060	0.040	0.003	0.013
30	0.040	0.176	0.176	0.152	-----	0.492	0.176	0.128	0.060	0.040	0.003	0.013
31	0.040	-----	0.176	0.176	-----	0.536	-----	0.080	-----	0.040	0.003	-----
Maks.	0.040	0.176	0.264	0.200	0.232	3.90	0.536	0.840	0.360	0.104	0.128	0.080
Min.	0.013	0.040	0.128	0.152	0.128	0.232	0.080	0.080	0.060	0.040	0.003	0.003
Ortalama	0.023	0.107	0.191	0.183	0.204	1.39	0.270	0.277	0.113	0.044	0.035	0.009
LT/SN/Km2	0.073	0.342	0.611	0.584	0.651	4.43	0.863	0.885	0.362	0.140	0.112	0.030
AKIM mm.	0.196	0.887	1.64	1.56	1.58	11.9	2.24	2.37	0.939	0.375	0.300	0.078
MİL. M3	0.061	0.278	0.512	0.490	0.494	3.72	0.701	0.743	0.294	0.118	0.094	0.024

SU YILI (2006) YILLIK TOPLAM AKIM 7.53 MİLYON M3 24 MM. 0.8 LT/SN/Km2

15. Kizilırmak Havzasi

D15A093 DEVRES ÇAYI ÇUKURCA

YERİ : **KURŞUNLU-HOCAHASAN YOLUNUN 8 KM.SİNDEKI ÇUKURCA KÖYÜNÜN IÇINDEDIR**
33°19'12" Doğu - 40°48'46" Kuzey

YAĞIŞ ALANI : **913.30 km2** **YAKLAŞIK KOT : 1007 m**

GÖZLEM SÜRESİ : **23.07.1965 - 30.09.2006**

ORTALAMA AKIMLAR : **Gözlem süresinde 4.348 4.417 m3/sn. (36 Yıllık) 2006 Su yılında 3.613 m3/sn.**

ANLIK EN ÇOK VE EN AZ AKIMLAR:

2006 Su yılında anlık ençok akım	**:**	**70.2**	**m3/sn**	**03.03.2006**
2006 Su yılında anlık enaz akım	**:**	**0.440**	**m3/sn**	**07.02.2006**
Gözlem süresinde anlık ençok akım	**:**	**380.**	**m3/sn**	**27.03.1980**
Gözlem süresinde anlık enaz akım	**:**	**0.195**	**m3/sn**	**29.07.1981**

13. Anahtar Eğrisi (Seviyeler cm olarak)

Seviye	Akım	Seviye	Akım	Seviye	Akım	Seviye	Akım
46	0.050	70	3.7	150	72.0	200	156.
50	0.190	90	11.0	160	88.0	210	174.
54	0.540	110	25.0	170	105.	220	192.
56	0.740	130	45.0	180	122.	230	210.
60	1.5	140	58.0	190	139.	240	230.

Akımlar 01 Ekim 2005 'den 30 Eylül 2006' a kadar m3/sn olarak

Gün	Ekim	Kasım	Aralık	Ocak	Şubat	Mart	Nisan	Mayıs	Haziran	Temmuz	Ağustos	Eylül
01	2.00	2.20	2.00	1.60	1.40	16.4	11.6	2.40	2.86	2.63	1.40	1.26
02	1.80	2.20	2.00	2.00	1.40	23.8	10.7	2.40	3.09	2.63	1.40	1.60
03	2.20	2.20	2.00	1.80	1.60	36.6	9.35	2.63	2.86	2.40	1.40	1.60
04	2.20	2.40	2.00	1.80	1.60	28.2	8.00	2.40	3.32	2.40	1.40	1.60
05	2.00	2.63	2.00	1.80	1.60	17.7	7.34	2.40	3.32	2.40	1.40	1.60
06	2.00	2.63	2.00	1.80	1.11	22.2	6.68	2.20	3.32	2.20	1.40	1.40
07	2.00	2.40	2.00	2.00	0.824	23.8	6.02	2.20	2.86	2.00	1.40	1.11
08	1.80	2.40	1.80	2.20	2.00	28.2	6.68	2.40	2.86	2.00	1.26	1.11
09	1.60	2.40	1.80	2.00	2.63	26.2	7.01	2.40	3.09	2.20	1.11	1.11
10	1.80	2.40	1.80	1.80	2.86	13.8	6.68	2.20	3.32	2.20	1.11	0.968
11	1.80	2.40	1.80	1.80	3.32	11.6	6.35	2.20	3.55	2.00	1.11	0.968
12	1.80	2.40	1.80	1.80	3.78	10.7	6.02	2.00	3.78	2.00	0.968	0.968
13	1.80	2.20	1.40	1.80	3.32	17.1	6.02	2.00	3.32	1.80	0.968	0.968
14	2.00	2.00	1.40	1.80	3.09	18.4	5.36	2.00	2.63	2.20	0.968	0.968
15	2.00	2.20	1.26	1.40	3.32	16.4	5.36	1.80	2.63	1.60	0.968	0.968
16	2.00	2.00	1.26	1.26	2.86	14.5	5.03	1.80	2.40	1.60	0.968	0.968
17	2.00	2.00	1.26	1.26	2.40	12.5	4.47	1.80	2.20	1.60	0.968	0.968
18	2.00	2.00	1.26	1.26	2.40	10.7	4.01	1.80	2.20	1.80	0.968	0.968
19	2.00	2.00	1.40	1.26	2.63	9.35	3.55	2.00	2.00	2.00	0.968	0.968
20	2.00	2.00	1.40	1.26	3.55	8.00	3.32	2.00	2.00	1.80	0.968	0.968
21	2.00	2.20	1.26	1.40	3.78	7.67	3.32	2.00	2.20	1.60	0.968	0.968
22	2.00	2.40	1.26	1.40	3.55	9.80	3.55	2.00	2.20	1.40	0.968	1.11
23	2.00	2.00	1.26	1.60	3.78	26.2	3.32	1.80	2.20	1.11	0.968	1.26
24	2.00	2.20	1.26	1.80	4.01	40.3	3.32	1.80	2.40	1.11	1.11	1.40
25	2.00	2.00	1.26	1.80	5.03	26.2	2.86	1.60	2.40	1.80	1.11	1.60
26	2.00	2.00	1.26	1.80	9.35	15.8	2.86	1.26	2.40	1.80	1.11	2.00
27	2.00	2.20	1.26	1.40	13.2	13.2	2.63	1.80	2.40	1.60	1.26	1.60
28	2.00	2.20	1.26	1.26	12.1	12.5	2.40	1.80	2.40	1.60	1.11	1.26
29	2.20	2.20	1.40	1.40	-----	12.1	2.20	1.80	2.40	1.60	1.11	1.11
30	2.20	2.00	1.60	1.40	-----	12.5	2.20	1.60	2.63	1.60	1.11	1.11
31	2.20	-----	1.80	1.40	-----	15.8	-----	1.80	-----	1.40	1.11	-----
Maks.	2.40	2.63	2.00	2.40	15.8	70.2	13.8	3.09	3.78	2.63	1.60	2.00
Min.	1.60	1.80	1.26	1.11	0.440	4.01	2.00	1.11	2.00	0.968	0.680	0.680
Ortalama	1.98	2.22	1.57	1.62	3.66	18.0	5.27	2.01	2.71	1.87	1.13	1.22
LT/SN/Km2	2.17	2.43	1.71	1.78	4.01	19.7	5.77	2.20	2.97	2.05	1.24	1.33
AKIM mm.	5.81	6.29	4.59	4.76	9.70	52.8	15.0	5.89	7.69	5.49	3.31	3.45
MİL. M3	5.30	5.74	4.19	4.35	8.86	48.2	13.7	5.38	7.02	5.02	3.03	3.15

SU YILI (2006) YILLIK TOPLAM AKIM 113.94 MİLYON M3 125 MM. 4.0 LT/SN/Km2

15. Kizilirmak Havzasi

D15A095 TARETÖZÜ D. YEŞİLYAZI

YERİ : **SULAKYURT-YEŞİLYAZI KÖYÜNÜN 11.KM SİNDEDIR.**
33°44'0" Doğu - 40°14'0" Kuzey

YAĞIŞ ALANI : **420.30 km2** **YAKLAŞIK KOT : 684 m**

GÖZLEM SÜRESİ : **11.08.1965 - 30.09.2006**

ORTALAMA AKIMLAR : **Gözlem süresinde 0.584 m3/sn. (19 Yıllık) 2006 Su yılında 0.333 m3/sn.**

ANLIK EN ÇOK VE EN AZ AKIMLAR:

2006 Su yılında anlık ençok akım	**:**	**7.15**	**m3/sn**	**11.06.2006**
2006 Su yılında anlık enaz akım	**:**	**0.048**	**m3/sn**	**01.10.2005**
Gözlem süresinde anlık ençok akım	**:**	**72.0**	**m3/sn**	**18.06.1988**
Gözlem süresinde anlık enaz akım	**:**	**0.003**	**m3/sn**	**17.06.2005**

İstasyon için kullanılmış anahtar bulunamadı.

Akımlar 01 Ekim 2005 'den 30 Eylül 2006' a kadar m3/sn olarak

Gün	Ekim	Kasım	Aralık	Ocak	Şubat	Mart	Nisan	Mayıs	Haziran	Temmuz	Ağustos	Eylül
01	0.070	0.180	0.180	0.230	0.180	1.28	0.700	0.700	0.700	0.230	0.230	0.130
02	0.070	0.180	0.180	0.230	0.180	0.900	0.700	0.700	0.530	0.230	0.230	0.180
03	0.100	0.180	0.180	0.230	0.180	0.700	0.700	0.700	0.295	0.230	0.230	0.180
04	0.100	0.180	0.180	0.230	0.180	0.530	0.530	0.700	0.295	0.230	0.180	0.180
05	0.100	0.180	0.230	0.230	0.180	0.530	0.530	0.900	0.295	0.230	0.130	0.180
06	0.100	0.180	0.230	0.230	0.180	0.530	0.530	1.10	0.295	0.180	0.130	0.180
07	0.100	0.180	0.230	0.230	0.180	0.700	0.530	1.10	0.295	0.180	0.130	0.180
08	0.100	0.180	0.230	0.230	0.180	0.530	0.700	1.10	0.295	0.180	0.180	0.180
09	0.100	0.180	0.230	0.230	0.360	0.530	0.530	0.900	0.295	0.180	0.180	0.230
10	0.100	0.180	0.230	0.230	0.360	0.530	0.700	0.900	0.360	0.130	0.180	0.230
11	0.100	0.180	0.230	0.230	0.230	0.530	0.700	0.900	0.700	0.130	0.180	0.230
12	0.100	0.180	0.230	0.230	0.230	0.530	0.700	0.700	0.360	0.130	0.180	0.230
13	0.100	0.180	0.230	0.230	0.230	0.530	0.700	0.700	0.360	0.180	0.180	0.230
14	0.100	0.180	0.230	0.230	0.230	0.530	0.700	0.700	0.360	0.180	0.180	0.230
15	0.100	0.180	0.230	0.230	0.180	0.530	0.900	0.700	0.360	0.180	0.180	0.230
16	0.100	0.180	0.230	0.180	0.180	0.530	0.900	0.530	0.360	0.130	0.180	0.230
17	0.100	0.180	0.230	0.180	0.180	0.700	0.700	0.700	0.295	0.130	0.180	0.180
18	0.130	0.180	0.230	0.180	0.230	0.900	0.700	0.700	0.295	0.130	0.180	0.180
19	0.130	0.230	0.230	0.180	0.295	0.700	0.700	0.530	0.295	0.130	0.130	0.180
20	0.130	0.230	0.230	0.180	0.360	0.530	0.530	0.530	0.230	0.130	0.130	0.180
21	0.130	0.295	0.230	0.180	0.360	0.530	0.530	0.530	0.230	0.130	0.130	0.230
22	0.130	0.295	0.230	0.180	0.360	0.530	0.700	0.530	0.230	0.130	0.180	0.295
23	0.130	0.230	0.230	0.180	0.360	0.900	0.700	0.530	0.230	0.130	0.130	0.295
24	0.130	0.230	0.230	0.180	0.530	1.10	0.700	0.360	0.230	0.130	0.130	0.295
25	0.130	0.230	0.230	0.180	1.10	0.700	0.530	0.360	0.130	0.100	0.130	0.295
26	0.130	0.230	0.230	0.180	1.10	0.700	0.700	0.360	0.130	0.130	0.130	0.295
27	0.180	0.230	0.230	0.180	1.63	0.700	0.530	0.530	0.130	0.180	0.130	0.295
28	0.180	0.180	0.230	0.230	1.45	0.700	0.530	0.530	0.130	0.180	0.130	0.295
29	0.180	0.180	0.230	0.230	-----	0.700	0.530	0.700	0.130	0.180	0.130	0.295
30	0.180	0.180	0.230	0.180	-----	0.700	0.530	0.700	0.230	0.180	0.130	0.295
31	0.180	-----	0.230	0.180	-----	0.530	-----	0.700	-----	0.230	0.130	-----
Maks.	0.180	0.530	0.230	0.295	2.88	1.80	0.900	1.80	7.15	0.530	0.360	1.63
Min.	0.048	0.130	0.180	0.100	0.180	0.295	0.530	0.295	0.048	0.070	0.100	0.130
Ortalama	0.120	0.199	0.224	0.207	0.407	0.663	0.645	0.688	0.302	0.166	0.161	0.228
LT/SN/Km2	0.285	0.474	0.532	0.494	0.968	1.58	1.54	1.64	0.719	0.395	0.382	0.542
AKIM mm.	0.763	1.23	1.42	1.32	2.34	4.23	3.98	4.38	1.86	1.06	1.02	1.41
MİL. M3	0.321	0.517	0.599	0.556	0.985	1.78	1.67	1.84	0.784	0.445	0.430	0.591

SU YILI (2006) YILLIK TOPLAM AKIM 10.52 MİLYON M3 25 MM. 0.8 LT/SN/Km2

15. Kizilirmak Havzasi

D15A098 SÖĞÜTÖZÜ DERESİ YUVA

YERİ : ÇANKIRI-ORTA İLÇESİ KANLICA MAHALLESİNDEN 5 KM. DEN SONRAKİ YUVA KÖYÜNÜN İÇERİSİNDEDİR

33°2'0" Doğu - 40°36'0" Kuzey

YAĞIŞ ALANI : 48.50 km2 **YAKLAŞIK KOT** : 1296 m

GÖZLEM SÜRESİ : 04.09.1965 - 30.09.2006

ORTALAMA AKIMLAR : Gözlem süresinde 0.413 m3/sn. (35 Yıllık) 2006 Su yılında 0.313 m3/sn.

ANLIK EN ÇOK VE EN AZ AKIMLAR:

2006 Su yılında anlık ençok akım	:	7.00	m3/sn	03.03.2006
2006 Su yılında anlık enaz akım	:	0.031	m3/sn	15.01.2006
Gözlem süresinde anlık ençok akım	:	125.	m3/sn	12.03.1968
Gözlem süresinde anlık enaz akım	:	0.000	m3/sn	20.08.1976

8. Anahtar Eğrisi (Seviyeler cm olarak)

Seviye	Akım	Seviye	Akım	Seviye	Akım	Seviye	Akım
30	0.031	40	0.095	100	5.1	160	22.0
32	0.039	50	0.250	120	9.4	170	26.0
34	0.049	60	0.580	130	12.0	180	31.0
36	0.061	70	1.1	140	15.0	190	36.0
38	0.077	80	2.0	150	18.0	200	42.0

Akımlar 01 Ekim 2005 'den 30 Eylül 2006' a kadar m3/sn olarak

Gün	Ekim	Kasım	Aralık	Ocak	Şubat	Mart	Nisan	Mayıs	Haziran	Temmuz	Ağustos	Eylül
01	0.358	0.424	0.044	0.049	0.049	1.60	1.10	0.095	0.627	0.358	0.502	0.119
02	0.358	0.174	0.049	0.055	0.049	1.70	0.986	0.095	0.424	0.358	0.231	0.119
03	0.358	0.061	0.049	0.055	0.049	4.56	0.815	0.095	0.250	0.424	0.155	0.193
04	0.358	0.061	0.049	0.055	0.049	2.91	0.768	0.086	0.250	0.358	0.250	0.304
05	0.358	0.061	0.049	0.055	0.049	2.00	0.721	0.086	0.155	0.358	0.250	0.174
06	0.277	0.061	0.049	0.068	0.049	1.42	0.385	0.077	0.095	0.358	0.277	0.095
07	0.277	0.061	0.049	0.077	0.044	1.70	0.212	0.077	0.304	0.358	0.304	0.095
08	0.277	0.049	0.039	0.077	0.044	1.90	0.212	0.077	0.541	0.358	0.304	0.095
09	0.277	0.044	0.039	0.077	0.039	1.26	0.385	0.077	0.627	0.358	0.193	0.095
10	0.277	0.044	0.039	0.061	0.039	0.768	0.721	0.095	0.627	0.358	0.095	0.095
11	0.304	0.044	0.039	0.061	0.061	0.768	0.721	0.119	0.502	0.358	0.095	0.095
12	0.331	0.044	0.039	0.044	0.061	0.768	0.627	0.095	0.502	0.358	0.095	0.095
13	0.331	0.044	0.039	0.044	0.068	0.986	0.627	0.095	0.358	0.358	0.095	0.095
14	0.331	0.049	0.039	0.039	0.077	1.34	0.580	0.095	0.331	0.358	0.095	0.095
15	0.331	0.049	0.044	0.031	0.095	1.26	0.424	0.077	0.304	0.358	0.095	0.095
16	0.304	0.049	0.049	0.031	0.095	0.872	0.358	0.077	0.358	0.358	0.095	0.095
17	0.304	0.044	0.049	0.031	0.086	0.872	0.304	0.174	0.331	0.385	0.095	0.095
18	0.304	0.044	0.049	0.031	0.086	0.674	0.212	0.424	0.304	0.119	0.095	0.095
19	0.331	0.044	0.049	0.031	0.086	0.502	0.131	0.502	0.331	0.143	0.095	0.095
20	0.331	0.077	0.049	0.031	0.086	0.502	0.131	0.502	0.358	0.119	0.095	0.143
21	0.331	0.119	0.049	0.039	0.086	0.674	0.119	0.463	0.358	0.131	0.095	0.212
22	0.331	0.095	0.049	0.039	0.061	1.10	0.119	0.424	0.358	0.231	0.095	0.212
23	0.304	0.068	0.044	0.039	0.068	1.80	0.131	0.424	0.358	0.768	0.107	0.212
24	0.304	0.055	0.044	0.039	0.077	2.52	0.143	0.358	0.358	0.721	0.131	0.212
25	0.304	0.055	0.044	0.039	0.107	1.42	0.131	0.250	0.358	0.721	0.174	0.304
26	0.358	0.055	0.044	0.039	0.502	1.18	0.107	0.212	0.358	0.674	0.193	0.174
27	0.424	0.049	0.044	0.044	1.34	0.986	0.107	0.277	0.331	0.721	0.231	0.095
28	0.424	0.049	0.044	0.044	0.986	0.986	0.107	0.358	0.304	0.721	0.155	0.095
29	0.424	0.049	0.049	0.044	-----	1.04	0.095	0.212	0.304	0.580	0.095	0.086
30	0.424	0.044	0.049	0.049	-----	1.34	0.095	0.304	0.304	0.580	0.095	0.086
31	0.424	-----	0.049	0.049	-----	1.34	-----	0.627	-----	0.580	0.107	-----
Maks.	0.424	0.424	0.049	0.077	1.42	7.00	1.10	0.627	0.627	0.872	0.502	0.304
Min.	0.277	0.044	0.039	0.031	0.039	0.502	0.095	0.077	0.077	0.095	0.095	0.086
Ortalama	0.336	0.072	0.045	0.047	0.160	1.38	0.386	0.224	0.366	0.419	0.161	0.136
LT/SN/Km2	6.94	1.49	0.937	0.976	3.30	28.4	7.95	4.61	7.54	8.64	3.32	2.80
AKIM mm.	18.6	3.86	2.51	2.61	8.00	76.2	20.6	12.3	19.5	23.1	8.89	7.25
MİL. M3	0.901	0.187	0.122	0.127	0.388	3.69	1.000	0.599	0.948	1.12	0.431	0.352

SU YILI (2006) YILLIK TOPLAM AKIM 9.86 MİLYON M3 203 MM. 6.5 LT/SN/Km2

15. Kizilirmak Havzasi

D15A099 Kestovan S. Sarioglan Çiftligi

YERİ : 36°4'11" Doğu - 39°1'15" Kuzey

YAĞIŞ ALANI : 257,00 km2 **YAKLAŞIK KOT** : 1230 m

GÖZLEM SÜRESİ : 17.08.1965 - 30.09.2006

ORTALAMA AKIMLAR : Gözlem süresinde 0.732 m3/sn. (39 Yıllık) 2006 Su yılında 0.262 m3/sn.

ANLIK EN ÇOK VE EN AZ AKIMLAR:

2006 Su yılında anlık ençok akım	:	0.832	m3/sn	03.04.2006
2006 Su yılında anlık enaz akım	:	0.000	m3/sn	29.05.2006
Gözlem süresinde anlık ençok akım	:	105.	m3/sn	28.05.1968
Gözlem süresinde anlık enaz akım	:	0.000	m3/sn	05.08.1980

13. Anahtar Eğrisi (Seviyeler cm olarak)

Seviye	Akım	Seviye	Akım	Seviye	Akım	Seviye	Akım
1	0.000	11	0.265	31	2.6	61	8.9
3	0.001	13	0.395	36	3.4	71	11.2
5	0.023	15	0.540	41	4.4	81	13.5
7	0.080	21	1.2	46	5.4	91	15.8
9	0.160	26	1.8	51	6.6	101	18.1

Akımlar 01 Ekim 2005 'den 30 Eylül 2006' a kadar m3/sn olarak

Gün	Ekim	Kasım	Aralık	Ocak	Şubat	Mart	Nisan	Mayıs	Haziran	Temmuz	Ağustos	Eylül
01	KURU	0.470	0.470	0.470	0.395	0.395	0.620	0.620	KURU	KURU	KURU	KURU
02	KURU	0.470	0.470	0.470	0.395	0.395	0.726	0.160	KURU	KURU	KURU	KURU
03	KURU	0.470	0.470	0.265	0.395	0.395	0.832	0.330	KURU	KURU	KURU	KURU
04	KURU	0.470	0.265	0.470	0.330	0.620	0.726	0.832	KURU	KURU	KURU	KURU
05	KURU	0.470	0.265	0.470	0.330	0.620	0.620	0.470	KURU	KURU	KURU	KURU
06	KURU	0.470	0.210	0.470	0.330	0.620	0.620	0.395	KURU	KURU	KURU	KURU
07	KURU	0.470	0.210	0.470	0.330	0.620	0.395	0.330	KURU	KURU	KURU	KURU
08	KURU	0.470	0.265	0.470	0.395	0.540	0.330	0.395	KURU	KURU	KURU	KURU
09	KURU	0.470	0.265	0.470	0.395	0.620	0.265	0.470	KURU	KURU	KURU	KURU
10	0.117	0.470	0.265	0.470	0.470	0.620	0.210	0.470	KURU	KURU	KURU	KURU
11	0.117	0.470	0.265	0.470	0.470	0.620	0.265	0.470	KURU	KURU	KURU	KURU
12	0.160	0.470	0.330	0.470	0.470	0.620	0.210	0.330	KURU	KURU	KURU	KURU
13	0.160	0.470	0.395	0.470	0.470	0.540	0.210	0.395	KURU	KURU	KURU	KURU
14	0.265	0.470	0.395	0.470	0.540	0.620	0.395	0.470	KURU	KURU	KURU	KURU
15	0.265	0.470	0.395	0.470	0.470	0.620	0.330	0.330	KURU	KURU	KURU	KURU
16	0.265	0.395	0.395	0.470	0.470	0.540	0.330	0.330	KURU	KURU	KURU	KURU
17	0.265	0.395	0.395	0.470	0.470	0.620	0.470	0.330	KURU	KURU	KURU	KURU
18	0.265	0.470	0.395	0.470	0.470	0.620	0.265	0.470	KURU	KURU	KURU	KURU
19	0.330	0.470	0.395	0.470	0.470	0.620	0.210	0.395	KURU	KURU	KURU	KURU
20	0.330	0.470	0.395	0.470	0.470	0.620	0.117	0.395	KURU	KURU	KURU	KURU
21	0.330	0.470	0.395	0.470	0.470	0.620	0.023	0.395	KURU	KURU	KURU	KURU
22	0.330	0.540	0.395	0.470	0.470	0.620	0.023	0.210	KURU	KURU	KURU	KURU
23	0.395	0.470	0.395	0.470	0.470	0.620	0.023	0.210	KURU	KURU	KURU	KURU
24	0.470	0.470	0.395	0.470	0.470	0.620	0.023	0.160	KURU	KURU	KURU	KURU
25	0.470	0.470	0.395	0.470	0.540	0.620	0.023	0.117	KURU	KURU	KURU	KURU
26	0.470	0.470	0.395	0.470	0.540	0.620	0.023	0.048	KURU	KURU	KURU	KURU
27	0.470	0.470	0.395	0.470	0.540	0.620	0.023	0.023	KURU	KURU	KURU	KURU
28	0.470	0.470	0.395	0.395	0.620	0.620	0.048	0.005	KURU	KURU	KURU	KURU
29	0.470	0.470	0.395	0.395	-----	0.620	0.023	KURU	KURU	KURU	KURU	KURU
30	0.470	0.470	0.395	0.395	-----	0.620	0.023	KURU	KURU	KURU	KURU	KURU
31	0.470	-----	0.470	0.395	-----	0.620	-----	KURU	-----	KURU	KURU	-----
Maks.	0.470	0.540	0.470	0.470	0.620	0.620	0.832	0.832	KURU	KURU	KURU	KURU
Min.	0.470	0.395	0.210	0.265	0.330	0.395	0.023	KURU	KURU	KURU	KURU	KURU
Ortalama	0.237	0.467	0.365	0.454	0.452	0.590	0.280	0.308	KURU	KURU	KURU	KURU
LT/SN/Km2	0.923	1.82	1.42	1.77	1.76	2.30	1.09	1.20	0.000	0.000	0.000	0.000
AKIM mm.	2.47	4.71	3.81	4.73	4.25	6.15	2.82	3.21	0.000	0.000	0.000	0.000
MİL. M3	0.635	1.21	0.979	1.22	1.09	1.58	0.726	0.826	0.000	0.000	0.000	0.000

SU YILI (2006) YILLIK TOPLAM AKIM 8.27 MİLYON M3 32 MM. 1.0 LT/SN/Km2

15. Kizilirmak Havzasi

D15A107 İÇİN DERESİ YUVA

YERİ : **ORTA İLÇESİNDEN 8 KM. İLERİDEKİ YUVA KÖYÜNDEDİR.**
33°1'31" Doğu - 40°36'51" Kuzey

YAĞIŞ ALANI : **140.70 km2** **YAKLAŞIK KOT : 1299 m**

GÖZLEM SÜRESİ : **25.05.1966 - 30.09.2006**

ORTALAMA AKIMLAR : **Gözlem süresinde 1.165 m3/sn. (35 Yıllık) 2006 Su yılında 0.803 m3/sn.**

ANLIK EN ÇOK VE EN AZ AKIMLAR:

2006 Su yılında anlık ençok akım	:	**7.50**	**m3/sn**	**01.02.2006**
2006 Su yılında anlık enaz akım	:	**0.098**	**m3/sn**	**29.08.2006**
Gözlem süresinde anlık ençok akım	:	**75.0**	**m3/sn**	**12.03.1968**
Gözlem süresinde anlık enaz akım	:	**0.000**	**m3/sn**	**17.07.1968**

8. Anahtar Eğrisi (Seviyeler cm olarak)

Seviye	Akım	Seviye	Akım	Seviye	Akım	Seviye	Akım
44	0.010	60	0.700	110	7.8	160	18.4
46	0.028	70	1.6	120	9.7	170	21.0
48	0.060	80	2.8	130	11.6		
50	0.125	90	4.4	140	13.7		
55	0.330	100	6.1	150	16.0		

Akımlar 01 Ekim 2005 'den 30 Eylül 2006' a kadar m3/sn olarak

Gün	Ekim	Kasım	Aralık	Ocak	Şubat	Mart	Nisan	Mayıs	Haziran	Temmuz	Ağustos	Eylül
01	0.538	0.484	0.592	0.430	7.33	1.04	1.38	0.348	1.91	1.38	0.592	0.484
02	0.538	0.538	0.592	0.389	6.80	1.13	1.38	0.348	1.91	1.38	0.955	0.484
03	0.538	1.04	0.538	0.389	5.75	1.13	1.21	0.348	1.91	1.47	1.21	0.484
04	0.538	1.04	0.538	0.389	3.39	1.04	1.13	0.307	1.91	1.21	0.955	0.484
05	0.538	1.04	0.538	0.389	1.38	1.04	0.955	0.307	2.15	1.04	0.955	0.266
06	0.538	1.04	0.538	0.389	0.955	0.955	0.700	0.307	1.91	1.04	0.955	0.098
07	0.538	1.04	0.538	0.389	0.955	1.04	0.700	0.348	1.47	1.04	0.870	0.190
08	0.538	1.04	0.538	0.389	0.955	1.13	0.700	0.389	1.47	1.04	0.785	0.190
09	0.538	1.04	0.307	0.389	0.870	1.04	0.700	0.389	1.47	1.04	0.484	0.155
10	0.538	1.04	0.127	0.389	0.870	1.04	0.785	0.348	1.47	1.04	0.225	0.155
11	0.538	0.870	0.127	0.484	0.955	0.870	0.785	0.348	1.91	1.04	0.225	0.155
12	0.538	0.646	0.127	0.484	0.955	0.870	0.700	0.307	1.91	1.04	0.225	0.155
13	0.538	0.646	0.127	0.484	1.04	0.870	0.700	0.307	1.38	1.04	0.266	0.155
14	0.538	0.646	0.127	0.484	1.47	0.955	0.700	0.307	0.955	1.04	0.538	0.155
15	0.538	0.646	0.127	0.646	1.55	0.955	0.646	0.389	0.955	1.04	0.538	0.155
16	0.538	0.646	0.127	0.646	1.55	0.870	0.592	0.348	0.955	1.04	0.484	0.155
17	0.538	0.646	0.127	0.646	1.38	0.870	0.592	0.307	0.955	1.21	0.592	0.155
18	0.538	0.646	0.127	0.646	1.04	0.700	0.538	0.307	0.870	1.04	0.538	0.155
19	0.538	0.646	0.127	0.646	1.04	0.700	0.484	0.307	1.13	1.21	0.484	0.155
20	0.538	0.646	0.127	0.700	0.870	0.700	0.484	0.225	1.38	1.13	0.484	0.155
21	0.538	0.646	0.127	0.700	0.870	0.700	0.484	0.225	1.38	0.389	0.484	0.190
22	0.538	0.592	0.225	0.700	0.785	0.870	0.484	0.225	1.38	0.430	0.538	0.190
23	0.538	0.592	0.484	0.700	0.646	1.13	0.430	0.225	1.38	0.484	0.538	0.190
24	0.538	0.592	1.04	0.700	0.592	1.67	0.430	0.225	1.38	0.538	0.484	0.190
25	0.538	0.592	1.13	0.870	0.646	1.55	0.430	0.646	1.38	0.538	0.484	0.389
26	0.538	0.592	1.38	0.870	0.785	1.47	0.430	1.38	1.38	0.538	0.484	0.389
27	0.538	0.592	1.55	0.870	0.955	1.30	0.389	1.04	1.38	0.592	0.484	0.480
28	0.538	0.592	1.04	0.870	0.870	1.30	0.389	0.700	1.38	0.592	0.484	0.310
29	0.538	0.592	0.484	0.870	-----	1.38	0.348	0.700	1.38	0.592	0.266	0.310
30	0.538	0.592	0.430	3.23	-----	1.55	0.348	1.30	1.38	0.592	0.098	0.310
31	0.538	-----	0.430	7.15	-----	1.55	-----	1.91	-----	0.592	0.266	-----
Maks.	0.538	1.13	1.79	7.15	7.50	1.79	1.38	1.91	2.39	1.47	1.38	0.484
Min.	0.484	0.389	0.127	0.389	0.538	0.646	0.348	0.225	0.870	0.348	0.098	0.098
Ortalama	0.538	0.733	0.466	0.882	1.69	1.08	0.667	0.489	1.46	0.916	0.547	0.250
LT/SN/Km2	3.82	5.21	3.31	6.27	12.0	7.66	4.74	3.48	10.4	6.51	3.89	1.77
AKIM mm.	10.2	13.5	8.86	16.8	29.0	20.5	12.3	9.31	26.9	17.4	10.4	4.60
MİL. M3	1.44	1.90	1.25	2.36	4.08	2.89	1.73	1.31	3.78	2.45	1.47	0.647

SU YILI (2006) YILLIK TOPLAM AKIM 25.31 MİLYON M3 180 MM. 5.7 LT/SN/Km2

15. Kizilirmak Havzasi

D15A112 Degirmen D. Karacaören

YERİ : **1985KAYSERİ SİVAS YOLUNUN 45.5 KM.SİNDEN SAĞA AYRILAN İĞDECİKKÖY YOLUNUN 7.KM SİNDEKİ KARACAÖREN KÖYÜNDEDİR.**
35°57'54" Doğu - 38°57'50" Kuzey

YAĞIŞ ALANI : **175,80 km2** **YAKLAŞIK KOT : 1211 m**

GÖZLEM SÜRESİ : **04.07.1966 - 30.09.2006**

ORTALAMA AKIMLAR : **Gözlem süresinde 0.363 m3/sn. (37 Yıllık) 2006 Su yılında 0.061 m3/sn.**

ANLIK EN ÇOK VE EN AZ AKIMLAR:

2006 Su yılında anlık ençok akım	**:**	**20.1**	**m3/sn**	**23.09.2006**
2006 Su yılında anlık enaz akım	**:**	**0.001**	**m3/sn**	**28.08.2006**
Gözlem süresinde anlık ençok akım	**:**	**90.0**	**m3/sn**	**02.07.1979**
Gözlem süresinde anlık enaz akım	**:**	**0.000**	**m3/sn**	**10.08.1985**

İstasyon için kullanılmış anahtar bulunamadı.

Akımlar 01 Ekim 2005 'den 30 Eylül 2006' a kadar m3/sn olarak

Gün	Ekim	Kasım	Aralık	Ocak	Şubat	Mart	Nisan	Mayıs	Haziran	Temmuz	Ağustos	Eylül
01	0.034	0.048	0.067	0.067	0.067	0.092	0.092	0.092	0.048	0.023	0.005	0.003
02	0.034	0.092	0.067	0.067	0.067	0.092	0.160	0.120	0.048	0.023	0.005	0.003
03	0.048	0.092	0.092	0.067	0.067	0.092	0.160	0.200	0.048	0.023	0.005	0.005
04	0.048	0.092	0.092	0.067	0.067	0.092	0.160	0.250	0.048	0.023	0.005	0.005
05	0.048	0.092	0.092	0.067	0.067	0.092	0.160	0.160	0.048	0.023	0.005	0.008
06	0.048	0.092	0.092	0.067	0.092	0.092	0.120	0.120	0.048	0.023	0.005	0.005
07	0.048	0.092	0.092	0.067	0.092	0.092	0.120	0.092	0.034	0.023	0.005	0.005
08	0.048	0.067	0.092	0.067	0.092	0.092	0.120	0.092	0.034	0.023	0.003	0.003
09	0.048	0.092	0.092	0.067	0.092	0.092	0.092	0.092	0.034	0.023	0.003	0.003
10	0.048	0.067	0.092	0.067	0.092	0.092	0.092	0.092	0.034	0.023	0.005	0.003
11	0.048	0.067	0.092	0.067	0.092	0.092	0.092	0.092	0.034	0.023	0.003	0.003
12	0.048	0.067	0.092	0.067	0.092	0.092	0.092	0.092	0.034	0.023	0.003	0.003
13	0.048	0.067	0.092	0.067	0.092	0.092	0.067	0.092	0.034	0.023	0.005	0.003
14	0.048	0.067	0.092	0.067	0.092	0.092	0.067	0.092	0.034	0.023	0.005	0.003
15	0.048	0.067	0.092	0.067	0.092	0.092	0.067	0.092	0.034	0.023	0.005	0.003
16	0.048	0.067	0.120	0.067	0.092	0.092	0.067	0.092	0.034	0.014	0.005	0.003
17	0.048	0.067	0.120	0.067	0.092	0.092	0.067	0.092	0.034	0.014	0.003	0.003
18	0.048	0.067	0.120	0.067	0.092	0.092	0.067	0.092	0.034	0.014	0.008	0.003
19	0.067	0.067	0.120	0.067	0.092	0.092	0.067	0.092	0.034	0.014	0.034	0.003
20	0.067	0.067	0.120	0.067	0.092	0.092	0.067	0.092	0.034	0.014	0.014	0.003
21	0.048	0.067	0.120	0.067	0.092	0.092	0.067	0.092	0.034	0.014	0.008	0.003
22	0.048	0.067	0.120	0.067	0.092	0.092	0.067	0.092	0.034	0.014	0.005	0.008
23	0.048	0.067	0.120	0.067	0.092	0.092	0.067	0.092	0.034	0.008	0.005	0.310
24	0.048	0.067	0.067	0.067	0.092	0.092	0.092	0.092	0.023	0.008	0.003	0.120
25	0.048	0.067	0.067	0.067	0.092	0.092	0.092	0.092	0.023	0.005	0.003	0.014
26	0.048	0.067	0.067	0.067	0.092	0.092	0.092	0.092	0.023	0.005	0.003	0.014
27	0.048	0.067	0.067	0.067	0.092	0.092	0.092	0.092	0.023	0.005	0.005	0.014
28	0.048	0.067	0.067	0.067	0.092	0.092	0.092	0.092	0.034	0.005	0.003	0.014
29	0.048	0.067	0.067	0.067	-----	0.092	0.092	0.067	0.034	0.005	0.003	0.014
30	0.048	0.067	0.067	0.067	-----	0.092	0.092	0.067	0.034	0.005	0.003	0.014
31	0.048	-----	0.067	0.067	-----	0.092	-----	0.067	-----	0.005	0.003	-----
Maks.	0.250	0.092	0.120	0.067	0.092	0.092	0.160	0.370	0.048	0.023	0.048	20.1
Min.	0.014	0.014	0.067	0.067	0.067	0.092	0.067	0.067	0.023	0.003	0.001	0.003
Ortalama	0.048	0.072	0.091	0.067	0.088	0.092	0.095	0.102	0.035	0.016	0.006	0.020
LT/SN/Km2	0.275	0.411	0.519	0.381	0.498	0.523	0.539	0.581	0.201	0.091	0.032	0.113
AKIM mm.	0.736	1.06	1.39	1.02	1.20	1.40	1.40	1.56	0.521	0.243	0.086	0.294
MİL. M3	0.129	0.187	0.244	0.179	0.212	0.246	0.245	0.274	0.092	0.043	0.015	0.052

SU YILI (2006) YILLIK TOPLAM AKIM 1.92 MİLYON M3 11 MM. 0.3 LT/SN/Km2

15. Kizilirmak Havzasi

D15A115 SÖĞÜTÖZÜ DERESİ TAHTAKÖPRÜ

YERİ : **ANKARA-KONYA YOLUNDAN BALA İLÇESİNE DÖNÜLDÜKTEN YAKLAŞIK 20 KM. SONRA KÖPRÜNÜN SAĞ TARAFINDA SÖĞÜTÖZÜ DERESİNİN ÜZERİNDEDİR.**
32°58'29" Doğu - 40°6'58" Kuzey

YAĞIŞ ALANI : **73.00 km2** **YAKLAŞIK KOT : 1074 m**

GÖZLEM SÜRESİ : **29.07.1966 - 30.09.2006**

ORTALAMA AKIMLAR : **Gözlem süresinde 0.100 m3/sn. (4 Yıllık) 2006 Su yılında 0.131 m3/sn.**

ANLIK EN ÇOK VE EN AZ AKIMLAR:

2006 Su yılında anlık ençok akım	:	**3.75**	**m3/sn**	**02.03.2006**
2006 Su yılında anlık enaz akım	:	**0.015**	**m3/sn**	**22.10.2005**
Gözlem süresinde anlık ençok akım	:	**3.86**	**m3/sn**	**01.06.2005**
Gözlem süresinde anlık enaz akım	:	**0.000**	**m3/sn**	**23.10.2003**

İstasyon için kullanılmış anahtar bulunamadı.

Akımlar 01 Ekim 2005 'den 30 Eylül 2006' a kadar m3/sn olarak

Gün	Ekim	Kasım	Aralık	Ocak	Şubat	Mart	Nisan	Mayıs	Haziran	Temmuz	Ağustos	Eylül
01	0.024	0.024	0.037	0.037	0.052	0.960	0.290	0.125	0.096	0.071	0.052	0.037
02	0.024	0.024	0.037	0.037	0.052	1.93	0.290	0.125	0.096	0.071	0.037	0.071
03	0.024	0.024	0.037	0.037	0.052	1.47	0.200	0.125	0.096	0.125	0.037	0.052
04	0.024	0.024	0.037	0.052	0.052	1.28	0.200	0.125	0.096	0.125	0.037	0.037
05	0.024	0.024	0.024	0.052	0.052	1.20	0.160	0.125	0.071	0.125	0.037	0.037
06	0.024	0.037	0.024	0.052	0.052	0.748	0.160	0.125	0.096	0.125	0.037	0.037
07	0.024	0.037	0.024	0.052	0.052	0.748	0.160	0.125	0.096	0.125	0.037	0.037
08	0.024	0.037	0.024	0.052	0.052	0.748	0.160	0.125	0.096	0.125	0.037	0.037
09	0.024	0.037	0.037	0.052	0.052	0.748	0.160	0.125	0.071	0.125	0.037	0.037
10	0.024	0.052	0.037	0.052	0.052	0.616	0.160	0.125	0.071	0.125	0.037	0.037
11	0.024	0.052	0.037	0.052	0.125	0.550	0.160	0.125	0.071	0.125	0.037	0.037
12	0.024	0.052	0.037	0.052	0.160	0.550	0.160	0.125	0.071	0.125	0.037	0.037
13	0.024	0.052	0.037	0.052	0.096	0.550	0.160	0.125	0.071	0.125	0.037	0.037
14	0.024	0.052	0.037	0.052	0.096	0.550	0.160	0.125	0.071	0.125	0.037	0.037
15	0.024	0.052	0.037	0.052	0.096	0.440	0.160	0.125	0.071	0.125	0.037	0.037
16	0.037	0.052	0.037	0.052	0.385	0.335	0.160	0.125	0.071	0.096	0.037	0.037
17	0.037	0.052	0.037	0.052	0.385	0.335	0.160	0.125	0.071	0.096	0.037	0.037
18	0.037	0.052	0.037	0.052	0.335	0.335	0.160	0.125	0.071	0.096	0.037	0.037
19	0.037	0.052	0.037	0.052	0.440	0.335	0.125	0.125	0.071	0.096	0.037	0.037
20	0.037	0.052	0.037	0.052	0.440	0.335	0.125	0.125	0.071	0.096	0.037	0.037
21	0.024	0.052	0.037	0.052	0.385	0.335	0.125	0.125	0.071	0.096	0.037	0.037
22	0.015	0.052	0.037	0.052	0.385	0.335	0.125	0.125	0.071	0.096	0.037	0.037
23	0.015	0.052	0.037	0.052	0.385	0.335	0.125	0.125	0.071	0.096	0.037	0.037
24	0.024	0.052	0.037	0.052	0.385	0.335	0.125	0.096	0.052	0.096	0.037	0.037
25	0.024	0.052	0.037	0.052	0.682	0.335	0.125	0.096	0.071	0.096	0.037	0.071
26	0.024	0.052	0.037	0.052	1.20	0.335	0.125	0.096	0.071	0.096	0.037	0.052
27	0.024	0.052	0.037	0.052	0.814	0.335	0.125	0.096	0.071	0.052	0.037	0.052
28	0.024	0.052	0.037	0.052	1.04	0.290	0.125	0.096	0.071	0.052	0.037	0.052
29	0.024	0.052	0.037	0.052	-----	0.290	0.125	0.096	0.071	0.052	0.037	0.071
30	0.024	0.052	0.037	0.052	-----	0.290	0.125	0.096	0.071	0.052	0.037	0.200
31	0.024	-----	0.037	0.052	-----	0.290	-----	0.096	-----	0.052	0.037	-----
Maks.	0.037	0.052	0.037	0.052	1.20	3.75	0.290	0.245	0.125	3.20	0.052	0.385
Min.	0.015	0.024	0.024	0.037	0.052	0.245	0.096	0.096	0.037	0.037	0.024	0.024
Ortalama	0.026	0.045	0.035	0.051	0.298	0.589	0.157	0.118	0.076	0.099	0.037	0.048
LT/SN/Km2	0.350	0.621	0.484	0.692	4.09	8.07	2.16	1.61	1.04	1.36	0.513	0.655
AKIM mm.	0.936	1.61	1.30	1.85	9.89	21.6	5.59	4.31	2.71	3.65	1.38	1.70
MİL. M3	0.068	0.118	0.095	0.135	0.722	1.58	0.408	0.315	0.198	0.266	0.100	0.124

SU YILI (2006) YILLIK TOPLAM AKIM 4.13 MİLYON M3 57 MM. 1.8 LT/SN/Km2

15. Kizilirmak Havzasi

D15A117 KIZILIRMAK AHMETHACI

YERİ : **SİVAS ZARA İLÇSEİ AHMETHACI KÖYÜ GİRİŞİNDEKİ KÖPRÜDEDİR**
39°54'0" Doğu - 37°50'0" Kuzey

YAĞIŞ ALANI : **693,42 km2** **YAKLAŞIK KOT : 1361 m**

GÖZLEM SÜRESİ : **10.12.1966 – 30.09.2006**

ORTALAMA AKIMLAR : **Gözlem süresinde 7.623 m3/sn. (36 Yıllık) 2006 Su yılında 9.272 m3/sn.**

ANLIK EN ÇOK VE EN AZ AKIMLAR:

2006 Su yılında anlık ençok akım	:	**155.**	**m3/sn**	**02.05.2006**
2006 Su yılında anlık enaz akım	:	**1.57**	**m3/sn**	**24.02.2006**
Gözlem süresinde anlık ençok akım	:	**310.**	**m3/sn**	**01.04.1978**
Gözlem süresinde anlık enaz akım	:	**0.006**	**m3/sn**	**21.02.1972**

Akımlar 01 Ekim 2005 'den 30 Eylül 2006' a kadar m3/sn olarak

Gün	Ekim	Kasım	Aralık	Ocak	Şubat	Mart	Nisan	Mayıs	Haziran	Temmuz	Ağustos	Eylül
01	3.12	2.48	3.56	3.56	3.56	5.68	34.8	44.8	18.1	3.78	2.69	2.48
02	3.12	2.69	3.78	3.34	3.56	4.84	36.6	85.6	17.6	3.56	2.48	2.48
03	3.12	2.69	3.78	3.12	3.56	3.78	28.8	62.4	16.7	3.34	2.48	2.48
04	3.34	2.69	3.78	3.56	3.56	6.80	28.2	44.1	16.7	3.34	2.48	2.48
05	3.12	3.12	3.78	3.56	3.56	6.80	29.4	40.2	16.7	3.34	2.48	2.48
06	3.12	3.12	3.78	3.56	3.56	7.82	28.2	36.0	16.2	3.56	2.48	2.48
07	3.12	3.12	3.78	3.78	3.56	10.3	29.4	36.0	16.7	3.78	2.48	2.48
08	3.12	2.90	3.56	3.56	3.56	15.7	33.6	40.8	15.7	3.78	2.48	2.48
09	3.12	2.69	3.56	3.56	3.78	16.2	40.2	37.8	8.50	3.78	2.48	2.48
10	3.12	2.48	3.56	3.56	3.78	10.7	41.4	34.2	7.48	3.34	2.27	2.48
11	3.12	2.48	3.56	3.78	3.78	8.50	40.2	30.6	7.48	3.34	2.27	2.48
12	3.12	2.27	3.56	3.56	3.78	7.82	37.2	28.2	7.14	3.34	2.27	2.48
13	3.12	2.27	3.56	3.78	3.78	8.16	37.8	28.8	7.14	3.34	2.27	2.48
14	3.12	2.06	3.56	3.56	3.78	10.3	37.8	29.4	6.80	3.34	2.27	2.48
15	3.12	2.06	3.56	3.56	3.78	15.7	37.8	27.6	6.80	3.34	2.27	2.48
16	3.34	2.06	3.78	3.56	3.78	11.9	35.4	26.4	6.80	3.12	2.27	2.48
17	4.84	2.06	3.56	3.56	4.28	11.5	31.8	26.4	6.52	2.90	2.27	2.48
18	4.00	2.06	3.56	3.56	4.00	9.94	28.8	25.8	6.52	2.90	2.27	2.48
19	4.56	2.06	3.56	3.56	3.12	9.58	27.0	24.6	6.24	2.90	2.48	2.48
20	4.00	2.06	3.78	3.56	2.27	8.86	27.0	24.0	5.12	2.90	2.48	2.48
21	3.78	2.06	3.78	3.56	2.27	8.16	26.4	23.5	3.78	2.90	2.48	2.48
22	3.78	3.56	3.78	3.56	2.27	8.86	25.2	23.0	3.78	2.90	2.48	2.48
23	3.78	3.56	3.78	3.56	2.90	11.5	26.4	22.5	3.78	2.90	2.48	2.48
24	3.56	3.56	3.78	3.56	2.69	16.2	53.9	20.0	3.56	2.90	2.48	2.69
25	3.56	3.56	3.78	3.56	2.69	33.6	39.6	19.5	3.34	2.90	2.48	2.69
26	2.27	3.56	3.78	3.56	2.90	26.4	31.2	21.5	3.34	2.90	2.48	2.69
27	1.85	3.56	3.56	3.56	3.34	20.5	28.2	21.5	3.34	2.90	2.48	2.69
28	1.85	3.56	3.56	3.56	4.00	20.0	25.8	20.5	3.78	2.90	2.48	2.69
29	1.85	3.56	3.56	3.78	-----	20.0	26.4	20.5	3.78	2.90	2.48	2.90
30	1.85	3.56	3.56	4.00	-----	21.5	51.1	20.5	3.78	2.90	2.48	2.90
31	2.27	-----	3.56	4.28	-----	28.8	-----	20.0	-----	2.69	2.48	-----
Maks.	5.96	3.78	3.78	4.84	5.12	43.4	128.	155.	18.1	3.78	2.69	2.90
Min.	1.85	1.85	3.34	2.48	1.57	3.12	16.2	17.6	3.34	2.69	2.27	2.48
Ortalama	3.17	2.78	3.66	3.60	3.41	13.1	33.5	31.2	8.44	3.18	2.43	2.54
LT/SN/Km2	4.57	4.01	5.28	5.20	4.92	18.9	48.3	45.0	12.2	4.59	3.50	3.67
AKIM mm.	12.2	10.4	14.1	13.9	11.9	50.6	125.	120.	31.5	12.3	9.37	9.51
MİL. M3	8.48	7.22	9.80	9.65	8.25	35.1	86.9	83.5	21.9	8.53	6.50	6.59

SU YILI (2006) YILLIK TOPLAM AKIM 292.42 MİLYON M3 422 MM. 13.4 LT/SN/Km2

15. Kizilirmak Havzasi

D15A126 AKDERE OĞULCUK

YERİ : **BOĞAZLIYAN SARIPINAR DEVECİPINAR YOLUNDAN SAĞA AYRILANYOL ÜZERİNDEKİ OGULCUK KÖYÜNDEDİR**

35°20'47" Doğu - 39°7'8" Kuzey

YAĞIŞ ALANI : **289,00 km2** **YAKLAŞIK KOT : 1129 m**

GÖZLEM SÜRESİ : **16.08.1967 - 30.09.2006**

ORTALAMA AKIMLAR : **Gözlem süresinde 0.555 m3/sn. (27 Yıllık) 2006 Su yılında 0.140 m3/sn.**

ANLIK EN ÇOK VE EN AZ AKIMLAR:

2006 Su yılında anlık ençok akım	**:**	**0.434**	**m3/sn**	**03.04.2006**
2006 Su yılında anlık enaz akım	**:**	**0.000**	**m3/sn**	**01.10.2005**
Gözlem süresinde anlık ençok akım	**:**	**16.0**	**m3/sn**	**13.05.1968**
Gözlem süresinde anlık enaz akım	**:**	**0.000**	**m3/sn**	**22.12.1972**

19. Anahtar Eğrisi (Seviyeler cm olarak)

Seviye	Akım	Seviye	Akım	Seviye	Akım	Seviye	Akım
1	0.010	40	1.2	140	5.6	240	12.0
3	0.051	60	2.1	160	6.6	250	12.9
5	0.104	80	2.9	180	7.8	260	13.8
15	0.395	100	3.7	200	9.2	270	14.9
25	0.724	120	4.6	220	10.5	280	16.0

Akımlar 01 Ekim 2005 'den 30 Eylül 2006' a kadar m3/sn olarak

Gün	Ekim	Kasım	Aralık	Ocak	Şubat	Mart	Nisan	Mayıs	Haziran	Temmuz	Ağustos	Eylül
01	KURU	0.127	0.211	0.188	0.224	0.321	0.379	0.119	0.086	KURU	KURU	KURU
02	KURU	0.127	0.211	0.211	0.243	0.321	0.407	0.136	0.044	KURU	KURU	KURU
03	KURU	0.146	0.211	0.211	0.243	0.321	0.434	0.153	0.036	KURU	KURU	KURU
04	KURU	0.146	0.211	0.211	0.243	0.321	0.407	0.178	0.028	KURU	KURU	KURU
05	KURU	0.146	0.211	0.211	0.224	0.340	0.407	0.203	0.020	KURU	KURU	KURU
06	KURU	0.146	0.188	0.211	0.224	0.340	0.379	0.203	0.005	KURU	KURU	KURU
07	KURU	0.146	0.188	0.211	0.224	0.340	0.360	0.203	0.001	KURU	KURU	KURU
08	KURU	0.146	0.188	0.211	0.262	0.340	0.360	0.277	0.059	KURU	KURU	KURU
09	KURU	0.146	0.188	0.211	0.282	0.340	0.360	0.307	0.025	KURU	KURU	KURU
10	KURU	0.127	0.188	0.211	0.282	0.340	0.360	0.307	0.014	KURU	KURU	KURU
11	KURU	0.096	0.211	0.211	0.282	0.340	0.360	0.307	0.010	KURU	KURU	KURU
12	KURU	0.096	0.211	0.211	0.262	0.340	0.360	0.307	0.042	KURU	KURU	KURU
13	KURU	0.096	0.211	0.211	0.243	0.340	0.360	0.307	0.042	KURU	KURU	KURU
14	KURU	0.108	0.211	0.187	0.224	0.340	0.360	0.307	0.035	KURU	KURU	KURU
15	KURU	0.108	0.211	0.206	0.224	0.340	0.278	0.277	0.014	KURU	KURU	KURU
16	KURU	0.108	0.146	0.206	0.224	0.340	0.278	0.252	0.010	KURU	KURU	KURU
17	0.080	0.108	0.146	0.206	0.224	0.340	0.252	0.252	0.006	KURU	KURU	KURU
18	0.096	0.108	0.146	0.206	0.224	0.340	0.252	0.277	0.002	KURU	KURU	KURU
19	0.080	0.127	0.146	0.206	0.224	0.340	0.165	0.277	0.001	KURU	KURU	KURU
20	0.096	0.146	0.146	0.187	0.224	0.340	0.098	0.307	0.001	KURU	KURU	KURU
21	0.108	0.146	0.146	0.187	0.224	0.360	0.072	0.307	0.001	KURU	KURU	KURU
22	0.108	0.127	0.146	0.224	0.224	0.360	0.072	0.277	KURU	KURU	KURU	KURU
23	0.127	0.127	0.146	0.224	0.262	0.360	0.111	0.252	KURU	KURU	KURU	KURU
24	0.127	0.127	0.146	0.224	0.282	0.360	0.057	0.178	KURU	KURU	KURU	KURU
25	0.146	0.127	0.127	0.224	0.282	0.360	0.103	0.178	KURU	KURU	KURU	KURU
26	0.146	0.127	0.127	0.224	0.282	0.360	0.103	0.227	KURU	KURU	KURU	KURU
27	0.146	0.127	0.127	0.243	0.282	0.407	0.044	0.277	KURU	KURU	KURU	KURU
28	0.165	0.188	0.127	0.243	0.282	0.407	0.044	0.203	KURU	KURU	KURU	KURU
29	0.188	0.211	0.165	0.243	-----	0.379	0.103	0.153	KURU	KURU	KURU	KURU
30	0.188	0.211	0.188	0.243	-----	0.379	0.119	0.153	KURU	KURU	KURU	KURU
31	0.188	-----	0.188	0.243	-----	0.379	-----	0.119	-----	KURU	KURU	-----
Maks.	0.188	0.211	0.211	0.243	0.282	0.407	0.434	0.307	0.103	KURU	KURU	KURU
Min.	KURU	0.096	0.127	0.188	0.224	0.321	0.044	0.119	KURU	KURU	KURU	KURU
Ortalama	0.064	0.134	0.175	0.214	0.247	0.350	0.248	0.235	0.016	KURU	KURU	KURU
LT/SN/Km2	0.222	0.464	0.604	0.742	0.856	1.21	0.859	0.813	0.056	0.000	0.000	0.000
AKIM mm.	0.595	1.20	1.62	1.99	2.07	3.24	2.23	2.18	0.144	0.000	0.000	0.000
MİL. M3	0.172	0.348	0.468	0.574	0.598	0.936	0.643	0.629	0.042	0.000	0.000	0.000

SU YILI (2006) YILLIK TOPLAM AKIM 4.41 MİLYON M3 15 MM. 0.5 LT/SN/Km2

15. Kizilirmak Havzasi

D15A131 BAĞIRGANÖZÜ BAHADIN

YERİ : SORGUN SİVAS BAHADIN YOLUNUN 7.KM SİNDEKİ AKKÖPRÜDEDİR.
35°18'6" Doğu - 39°42'14" Kuzey

YAĞIŞ ALANI : 240,90 km2 **YAKLAŞIK KOT :** 1046 m

GÖZLEM SÜRESİ : 01.10.1967 - 30.09.2006

ORTALAMA AKIMLAR : Gözlem süresinde 0.703 m3/sn. (35 Yıllık) 2006 Su yılında 0.109 m3/sn.

ANLIK EN ÇOK VE EN AZ AKIMLAR:

2006 Su yılında anlık ençok akım	:	1.90	m3/sn	27.05.2006
2006 Su yılında anlık enaz akım	:	0.000	m3/sn	20.06.2006
Gözlem süresinde anlık ençok akım	:	25.0	m3/sn	02.05.1977
Gözlem süresinde anlık enaz akım	:	0.000	m3/sn	30.08.1997

11. Anahtar Eğrisi (Seviyeler cm olarak)

Seviye	Akım	Seviye	Akım	Seviye	Akım	Seviye	Akım
1	0.000	16	0.003	31	0.480	141	13.1
4	0.000	19	0.040	46	1.6	151	14.6
7	0.000	22	0.110	61	3.1	161	16.1
10	0.000	25	0.200	81	5.3	171	17.6
13	0.000	28	0.325	111	9.0		

Akımlar 01 Ekim 2005 'den 30 Eylül 2006' a kadar m3/sn olarak

Gün	Ekim	Kasım	Aralık	Ocak	Şubat	Mart	Nisan	Mayıs	Haziran	Temmuz	Ağustos	Eylül
01	0.070	0.110	0.140	0.140	0.088	0.200	0.170	0.170	0.170	KURU	KURU	KURU
02	0.070	0.110	0.140	0.140	0.088	0.200	0.170	0.240	0.140	KURU	KURU	KURU
03	0.088	0.140	0.140	0.140	0.088	0.200	0.170	0.325	0.140	0.001	KURU	KURU
04	0.088	0.140	0.140	0.140	0.088	0.170	0.170	0.200	0.110	0.003	KURU	KURU
05	0.088	0.140	0.140	0.200	0.088	0.170	0.170	0.170	0.088	0.003	KURU	KURU
06	0.088	0.140	0.140	0.200	0.170	0.170	0.170	0.170	0.088	0.003	KURU	KURU
07	0.088	0.140	0.140	0.200	0.170	0.170	0.140	0.170	0.088	0.003	KURU	KURU
08	0.088	0.140	0.140	0.200	0.170	0.170	0.170	0.170	0.088	0.003	KURU	KURU
09	0.088	0.140	0.140	0.200	0.240	0.170	0.170	0.170	0.088	0.003	KURU	KURU
10	0.088	0.140	0.140	0.200	0.280	0.140	0.170	0.170	0.088	0.003	KURU	KURU
11	0.088	0.140	0.140	0.200	0.280	0.140	0.140	0.170	0.088	0.003	KURU	KURU
12	0.088	0.140	0.140	0.200	0.280	0.140	0.140	0.170	0.088	0.001	KURU	KURU
13	0.088	0.140	0.140	0.200	0.240	0.140	0.140	0.170	0.088	KURU	KURU	KURU
14	0.088	0.140	0.140	0.200	0.240	0.140	0.170	0.170	0.070	KURU	KURU	KURU
15	0.088	0.140	0.140	0.200	0.240	0.170	0.170	0.170	0.022	KURU	0.170	KURU
16	0.088	0.110	0.140	0.200	0.240	0.170	0.170	0.170	0.005	KURU	0.240	KURU
17	0.088	0.110	0.140	0.200	0.280	0.170	0.170	0.170	0.003	KURU	KURU	KURU
18	0.088	0.140	0.140	0.088	0.280	0.170	0.140	0.170	0.001	KURU	KURU	KURU
19	0.088	0.140	0.140	0.088	0.280	0.170	0.140	0.170	KURU	KURU	KURU	KURU
20	0.088	0.170	0.140	0.088	0.280	0.170	0.140	0.170	KURU	KURU	KURU	KURU
21	0.088	0.170	0.140	0.088	0.280	0.170	0.140	0.170	KURU	KURU	KURU	KURU
22	0.088	0.170	0.140	0.088	0.240	0.170	0.140	0.140	KURU	KURU	KURU	KURU
23	0.088	0.170	0.140	0.088	0.240	0.170	0.140	0.140	KURU	KURU	KURU	KURU
24	0.088	0.140	0.140	0.088	0.240	0.170	0.140	0.110	KURU	KURU	KURU	KURU
25	0.110	0.140	0.140	0.088	0.200	0.170	0.140	0.110	KURU	KURU	KURU	KURU
26	0.110	0.140	0.140	0.088	0.200	0.170	0.140	0.110	KURU	KURU	KURU	KURU
27	0.110	0.140	0.140	0.088	0.200	0.170	0.140	0.780	KURU	KURU	KURU	KURU
28	0.110	0.140	0.140	0.088	0.200	0.170	0.140	0.600	KURU	KURU	KURU	KURU
29	0.110	0.140	0.140	0.088	-----	0.170	0.140	0.240	KURU	KURU	KURU	KURU
30	0.110	0.088	0.140	0.088	-----	0.170	0.170	0.200	KURU	KURU	KURU	KURU
31	0.110	-----	0.140	0.088	-----	0.170	-----	0.170	-----	KURU	KURU	-----
Maks.	0.110	0.170	0.140	0.200	0.280	0.200	0.170	1.90	0.170	0.003	0.280	KURU
Min.	0.070	0.088	0.140	0.088	0.088	0.140	0.140	0.110	KURU	KURU	KURU	KURU
Ortalama	0.092	0.138	0.140	0.142	0.211	0.168	0.154	0.207	0.048	0.001	0.013	KURU
LT/SN/Km2	0.381	0.574	0.581	0.588	0.876	0.698	0.639	0.860	0.201	0.003	0.055	0.000
AKIM mm.	1.02	1.49	1.56	1.58	2.12	1.87	1.66	2.30	0.521	0.009	0.147	0.000
MİL. M3	0.246	0.358	0.375	0.379	0.511	0.450	0.399	0.555	0.126	0.002	0.035	0.000

SU YILI (2006) YILLIK TOPLAM AKIM 3.44 MİLYON M3 14 MM. 0.5 LT/SN/Km2

15. Kizilirmak Havzasi

D15A133 TERME ÇAYI TÜNEY

YERİ : **ANKARA-KALECİK-ÇANKIRI YOLUNUN 75.KM'SİNDE TERME ÇAYI ÜZERINDEKI ESKI KÖPRÜNÜN 50 M. MENBASINDADIR.**
33°31'0" Doğu - 40°22'0" Kuzey

YAĞIŞ ALANI : **1326.90 km2** **YAKLAŞIK KOT : 687 m**

GÖZLEM SÜRESİ : **07.01.1967 - 30.09.2006**

ORTALAMA AKIMLAR : **Gözlem süresinde 2.452 m3/sn. (37 Yıllık) 2006 Su yılında 1.634 m3/sn.**

ANLIK EN ÇOK VE EN AZ AKIMLAR:

2006 Su yılında anlık ençok akım	:	**64.0**	**m3/sn**	**03.03.2006**
2006 Su yılında anlık enaz akım	:	**0.029**	**m3/sn**	**13.09.2006**
Gözlem süresinde anlık ençok akım	:	**185.**	**m3/sn**	**26.04.1964**
Gözlem süresinde anlık enaz akım	:	**0.000**	**m3/sn**	**12.08.1973**

İstasyon için kullanılmış anahtar bulunamadı.

Akımlar 01 Ekim 2005 'den 30 Eylül 2006' a kadar m3/sn olarak

Gün	Ekim	Kasım	Aralık	Ocak	Şubat	Mart	Nisan	Mayıs	Haziran	Temmuz	Ağustos	Eylül
01	0.350	0.440	0.530	0.440	0.440	12.8	5.28	0.924	0.280	0.280	0.080	0.049
02	0.280	0.440	0.530	0.440	0.440	20.5	4.92	0.924	0.280	0.440	0.080	0.063
03	0.350	0.440	0.530	0.440	0.440	38.0	4.56	1.07	0.220	0.530	0.080	0.063
04	0.350	0.530	0.530	0.440	0.440	28.3	4.20	1.07	0.220	0.440	0.063	0.063
05	0.350	0.640	0.530	0.440	0.530	14.9	4.20	1.21	0.170	0.440	0.063	0.063
06	0.350	0.530	0.440	0.440	0.530	14.3	3.86	1.21	0.135	0.440	0.049	0.063
07	0.350	0.530	0.440	0.440	0.530	14.3	3.86	1.35	0.105	0.440	0.049	0.063
08	0.350	0.530	0.440	0.440	0.530	14.3	3.52	1.58	0.105	0.350	0.080	0.063
09	0.350	0.530	0.440	0.440	0.530	16.4	3.18	1.35	0.105	0.280	0.080	0.063
10	0.350	0.530	0.440	0.440	0.530	13.3	2.50	1.35	0.105	0.220	0.063	0.063
11	0.350	0.530	0.440	0.440	0.640	10.9	2.50	1.21	0.105	0.220	0.063	0.049
12	0.350	0.530	0.440	0.440	1.07	8.90	2.50	1.21	0.135	0.220	0.063	0.037
13	0.350	0.530	0.440	0.440	0.782	7.92	2.50	1.21	0.135	0.135	0.063	0.029
14	0.350	0.530	0.440	0.440	0.782	9.40	2.50	1.21	0.170	0.105	0.063	0.049
15	0.280	0.530	0.440	0.440	0.640	13.8	2.50	1.21	0.220	0.105	0.063	0.049
16	0.350	0.530	0.440	0.440	0.640	11.4	2.27	1.07	0.280	0.105	0.063	0.063
17	0.350	0.530	0.440	0.440	0.640	9.40	2.04	0.924	0.170	0.080	0.063	0.063
18	0.440	0.530	0.440	0.440	0.530	8.90	1.81	0.924	0.135	0.105	0.063	0.063
19	0.350	0.530	0.440	0.440	0.530	8.40	1.58	0.924	0.135	0.105	0.063	0.063
20	0.440	0.530	0.440	0.440	0.640	7.92	1.58	0.782	0.105	0.105	0.063	0.063
21	0.440	0.530	0.440	0.440	0.782	7.44	1.58	0.640	0.105	0.105	0.063	0.063
22	0.440	0.530	0.440	0.440	0.924	7.44	1.58	0.440	0.105	0.105	0.063	0.063
23	0.440	0.530	0.440	0.440	1.07	8.90	1.35	0.350	0.080	0.105	0.063	0.135
24	0.440	0.530	0.440	0.440	1.35	12.8	1.35	0.350	0.080	0.080	0.063	0.170
25	0.440	0.530	0.440	0.440	2.04	11.9	1.21	0.350	0.063	0.080	0.063	0.350
26	0.350	0.530	0.440	0.440	4.92	9.40	1.21	0.350	0.063	0.105	0.049	0.350
27	0.350	0.530	0.440	0.440	12.3	7.92	1.21	0.350	0.063	0.105	0.049	0.440
28	0.350	0.530	0.440	0.640	9.90	7.44	1.07	0.350	0.063	0.105	0.049	0.440
29	0.350	0.530	0.440	0.640	-----	7.44	1.07	0.350	0.350	0.105	0.049	0.440
30	0.350	0.530	0.440	0.530	-----	7.44	0.924	0.350	0.220	0.105	0.049	0.440
31	0.350	-----	0.440	0.530	-----	5.64	-----	0.350	-----	0.105	0.049	-----
Maks.	0.440	0.782	0.530	0.640	16.9	64.0	5.64	1.81	0.440	0.640	0.350	0.530
Min.	0.280	0.440	0.280	0.350	0.440	5.64	0.782	0.350	0.063	0.063	0.049	0.029
Ortalama	0.366	0.525	0.455	0.459	1.61	12.2	2.48	0.869	0.150	0.202	0.062	0.135
LT/SN/Km2	0.276	0.395	0.343	0.346	1.21	9.18	1.87	0.655	0.113	0.152	0.047	0.101
AKIM mm.	0.738	1.02	0.917	0.926	2.94	24.6	4.85	1.75	0.293	0.407	0.125	0.263
MİL. M3	0.980	1.36	1.22	1.23	3.90	32.6	6.43	2.33	0.389	0.540	0.166	0.349

SU YILI (2006) YILLIK TOPLAM AKIM 51.49 MİLYON M3 39 MM. 1.2 LT/SN/Km2

15. Kizilirmak Havzasi

D15A136 YENİCE DERESİ TEKKE YENİCESI

YERİ : YOZGAT-BOGAZLIYAN YOLUNUN 31.KM SINDE OSMANPASA-TEKKEYENICESI YOLUNUN 1 KM MANSABINDADIR

34°59'1" Doğu - 39°40'14" Kuzey

YAĞIŞ ALANI : 65,00 km2 **YAKLAŞIK KOT :** 1069 m

GÖZLEM SÜRESİ : 01.10.2005 - 30.09.2006

ORTALAMA AKIMLAR : Gözlem süresinde 0.092 m3/sn. (1 Yıllık) 2006 Su yılında 0.092 m3/sn.

ANLIK EN ÇOK VE EN AZ AKIMLAR:

2006 Su yılında anlık ençok akım	:	0.556 m3/sn	21.04.2006
2006 Su yılında anlık enaz akım	:	0.009 m3/sn	02.09.2006
Gözlem süresinde anlık ençok akım	:	0.556 m3/sn	21.04.2006
Gözlem süresinde anlık enaz akım	:	0.009 m3/sn	02.09.2006

1. Anahtar Eğrisi (Seviyeler cm olarak)

Seviye	Akım	Seviye	Akım	Seviye	Akım	Seviye	Akım
4	0.003	22	0.387	60	4.3	100	11.4
6	0.005	30	0.852	70	5.9	110	13.4
9	0.009	38	1.5	80	7.6	120	15.4
13	0.070	40	1.8	82	8.0	130	17.4
17	0.176	50	3.0	90	9.4	140	19.4

Akımlar 01 Ekim 2005 'den 30 Eylül 2006' a kadar m3/sn olarak

Gün	Ekim	Kasım	Aralık	Ocak	Şubat	Mart	Nisan	Mayıs	Haziran	Temmuz	Ağustos	Eylül
01	0.023	0.023	0.023	0.023	0.047	0.257	0.343	0.343	0.152	0.023	0.016	0.016
02	0.023	0.023	0.023	0.023	0.047	0.257	0.343	0.298	0.152	0.023	0.016	0.009
03	0.023	0.023	0.023	0.023	0.047	0.257	0.343	0.257	0.152	0.016	0.016	0.016
04	0.023	0.023	0.023	0.023	0.047	0.257	0.343	0.217	0.152	0.016	0.016	0.016
05	0.023	0.023	0.023	0.023	0.047	0.257	0.298	0.176	0.152	0.016	0.016	0.016
06	0.023	0.023	0.023	0.023	0.047	0.257	0.257	0.152	0.099	0.016	0.016	0.016
07	0.023	0.023	0.023	0.023	0.047	0.257	0.257	0.152	0.099	0.016	0.016	0.016
08	0.023	0.023	0.023	0.023	0.047	0.257	0.257	0.152	0.099	0.016	0.016	0.016
09	0.023	0.023	0.023	0.023	0.047	0.257	0.257	0.152	0.099	0.016	0.016	0.016
10	0.023	0.023	0.023	0.023	0.047	0.298	0.257	0.152	0.099	0.016	0.016	0.016
11	0.023	0.023	0.023	0.023	0.047	0.298	0.257	0.152	0.099	0.016	0.016	0.016
12	0.023	0.023	0.023	0.023	0.047	0.298	0.257	0.152	0.099	0.023	0.016	0.016
13	0.023	0.023	0.023	0.023	0.047	0.343	0.257	0.176	0.099	0.023	0.016	0.016
14	0.023	0.023	0.023	0.023	0.047	0.343	0.257	0.176	0.099	0.023	0.016	0.016
15	0.023	0.023	0.023	0.023	0.047	0.343	0.257	0.152	0.099	0.023	0.016	0.016
16	0.023	0.023	0.023	0.023	0.070	0.343	0.217	0.152	0.099	0.023	0.016	0.016
17	0.023	0.023	0.023	0.023	0.099	0.343	0.217	0.152	0.099	0.023	0.016	0.016
18	0.023	0.023	0.023	0.023	0.099	0.343	0.257	0.152	0.099	0.023	0.016	0.016
19	0.023	0.023	0.023	0.023	0.127	0.343	0.217	0.152	0.099	0.023	0.016	0.016
20	0.023	0.023	0.023	0.023	0.152	0.343	0.257	0.152	0.099	0.016	0.016	0.016
21	0.023	0.023	0.023	0.023	0.152	0.387	0.343	0.152	0.070	0.016	0.016	0.016
22	0.023	0.023	0.023	0.047	0.176	0.387	0.217	0.152	0.099	0.016	0.016	0.016
23	0.023	0.023	0.023	0.047	0.176	0.387	0.217	0.152	0.099	0.016	0.016	0.016
24	0.023	0.023	0.023	0.047	0.176	0.387	0.217	0.152	0.099	0.016	0.016	0.016
25	0.023	0.023	0.023	0.047	0.217	0.387	0.217	0.152	0.099	0.016	0.016	0.016
26	0.023	0.023	0.023	0.047	0.257	0.343	0.217	0.152	0.099	0.016	0.016	0.016
27	0.023	0.023	0.023	0.047	0.217	0.343	0.217	0.152	0.099	0.016	0.016	0.016
28	0.023	0.023	0.023	0.047	0.257	0.343	0.217	0.152	0.070	0.016	0.016	0.016
29	0.023	0.023	0.023	0.047	-----	0.343	0.217	0.152	0.023	0.016	0.016	0.016
30	0.023	0.023	0.023	0.047	-----	0.343	0.217	0.152	0.023	0.016	0.016	0.016
31	0.023	-----	0.023	0.047	-----	0.343	-----	0.152	-----	0.016	0.016	-----
Maks.	0.023	0.023	0.023	0.047	0.343	0.387	0.556	0.387	0.152	0.023	0.016	0.016
Min.	0.023	0.023	0.023	0.023	0.047	0.176	0.127	0.127	0.023	0.016	0.016	0.009
Ortalama	0.023	0.023	0.023	0.031	0.103	0.321	0.257	0.171	0.101	0.018	0.016	0.016
LT/SN/Km2	0.354	0.354	0.354	0.473	1.58	4.93	3.95	2.63	1.55	0.281	0.246	0.243
AKIM mm.	0.948	0.917	0.948	1.27	3.83	13.2	10.2	7.03	4.02	0.752	0.659	0.629
MİL. M3	0.062	0.060	0.062	0.082	0.249	0.859	0.665	0.457	0.261	0.049	0.043	0.041

SU YILI (2006) YILLIK TOPLAM AKIM 2.89 MİLYON M3 44 MM. 1.4 LT/SN/Km2

15. Kizilirmak Havzasi

D15A137 YUSUFÖZÜ DERESİ BÜYÜK İNCİRLI

YERİ : YOZGAT BOGAZLIYAN YOLUNUN 25.KM SİNDEKİ DAR BOGAZDADIR
34°54'59" Doğu - 39°38'45" Kuzey

YAĞIŞ ALANI : 128,60 km2 **YAKLAŞIK KOT :** 1039 m

GÖZLEM SÜRESİ : 24.05.1968 - 30.09.2006

ORTALAMA AKIMLAR : Gözlem süresinde 0.391 m3/sn. (37 Yıllık) 2006 Su yılında 0.188 m3/sn.

ANLIK EN ÇOK VE EN AZ AKIMLAR:

2006 Su yılında anlık ençok akım	:	0.534	m3/sn	22.03.2006
2006 Su yılında anlık enaz akım	:	0.000	m3/sn	26.07.2006
Gözlem süresinde anlık ençok akım	:	185.	m3/sn	26.04.1964
Gözlem süresinde anlık enaz akım	:	0.000	m3/sn	12.08.1973

9. Anahtar Eğrisi (Seviyeler cm olarak)

Seviye	Akım	Seviye	Akım	Seviye	Akım	Seviye	Akım
1	0.000	11	0.066	21	0.390	81	6.9
3	0.000	13	0.110	31	0.920	101	10.8
5	0.005	15	0.165	41	1.7	121	15.3
7	0.016	17	0.230	51	2.7	131	17.9
9	0.036	19	0.310	61	3.8	141	20.5

Akımlar 01 Ekim 2005 'den 30 Eylül 2006' a kadar m3/sn olarak

Gün	Ekim	Kasım	Aralık	Ocak	Şubat	Mart	Nisan	Mayıs	Haziran	Temmuz	Ağustos	Eylül
01	0.005	0.270	0.368	0.425	0.110	0.270	0.438	0.270	0.087	0.050	KURU	KURU
02	0.005	0.270	0.368	0.425	0.110	0.270	0.438	0.310	0.110	0.050	KURU	KURU
03	0.005	0.270	0.368	0.425	0.110	0.270	0.438	0.310	0.087	0.050	KURU	KURU
04	0.010	0.270	0.310	0.425	0.110	0.270	0.438	0.310	0.087	0.036	KURU	KURU
05	0.005	0.270	0.310	0.425	0.110	0.270	0.390	0.310	0.066	0.036	KURU	KURU
06	0.005	0.310	0.310	0.425	0.110	0.270	0.390	0.310	0.066	0.036	KURU	KURU
07	0.005	0.368	0.310	0.425	0.135	0.270	0.350	0.310	0.066	0.036	KURU	KURU
08	0.005	0.425	0.310	0.425	0.135	0.270	0.390	0.310	0.066	0.036	KURU	KURU
09	0.005	0.425	0.310	0.425	0.135	0.270	0.390	0.310	0.066	0.025	KURU	KURU
10	0.005	0.483	0.310	0.483	0.135	0.270	0.350	0.310	0.066	0.036	KURU	KURU
11	0.005	0.483	0.310	0.483	0.165	0.270	0.350	0.310	0.066	0.016	KURU	KURU
12	0.072	0.368	0.425	0.483	0.230	0.270	0.350	0.270	0.087	0.005	KURU	KURU
13	0.072	0.368	0.368	0.110	0.270	0.270	0.310	0.270	0.087	0.005	KURU	KURU
14	0.072	0.368	0.368	0.110	0.230	0.270	0.270	0.270	0.087	0.005	KURU	KURU
15	0.104	0.368	0.368	0.110	0.230	0.270	0.350	0.230	0.110	0.002	KURU	KURU
16	0.104	0.368	0.425	0.110	0.230	0.270	0.350	0.230	0.087	0.002	KURU	KURU
17	0.140	0.368	0.425	0.110	0.200	0.270	0.350	0.230	0.087	0.002	KURU	KURU
18	0.140	0.368	0.425	0.110	0.230	0.230	0.350	0.230	0.087	0.002	KURU	KURU
19	0.176	0.368	0.368	0.110	0.230	0.270	0.350	0.200	0.066	0.002	KURU	KURU
20	0.176	0.368	0.368	0.110	0.230	0.310	0.310	0.230	0.066	KURU	KURU	KURU
21	0.176	0.483	0.368	0.110	0.230	0.350	0.270	0.200	0.066	KURU	KURU	KURU
22	0.176	0.368	0.368	0.110	0.230	0.390	0.270	0.165	0.066	KURU	KURU	KURU
23	0.176	0.368	0.368	0.110	0.230	0.390	0.310	0.135	0.050	KURU	KURU	KURU
24	0.176	0.368	0.310	0.110	0.230	0.390	0.270	0.135	0.050	KURU	KURU	KURU
25	0.229	0.368	0.310	0.110	0.230	0.438	0.310	0.135	0.050	KURU	KURU	KURU
26	0.229	0.368	0.368	0.110	0.230	0.486	0.310	0.165	0.050	KURU	KURU	KURU
27	0.229	0.425	0.368	0.110	0.270	0.486	0.270	0.165	0.050	KURU	KURU	KURU
28	0.229	0.425	0.368	0.110	0.270	0.486	0.270	0.165	0.050	KURU	KURU	KURU
29	0.270	0.425	0.368	0.110	-----	0.486	0.270	0.165	0.050	KURU	KURU	KURU
30	0.270	0.425	0.368	0.110	-----	0.486	0.270	0.165	0.050	KURU	KURU	KURU
31	0.270	-----	0.368	0.110	-----	0.438	-----	0.110	-----	KURU	KURU	-----
Maks.	0.368	0.483	0.425	0.483	0.270	0.534	0.534	0.350	0.110	0.066	KURU	KURU
Min.	0.005	0.003	0.310	0.110	0.110	0.200	0.230	0.087	0.050	KURU	KURU	KURU
Ortalama	0.114	0.373	0.357	0.238	0.192	0.330	0.339	0.233	0.071	0.014	KURU	KURU
LT/SN/Km2	0.889	2.90	2.77	1.85	1.49	2.57	2.64	1.81	0.552	0.108	0.000	0.000
AKIM mm.	2.38	7.51	7.43	4.95	3.60	6.87	6.83	4.86	1.43	0.290	0.000	0.000
MİL. M3	0.306	0.966	0.955	0.636	0.464	0.884	0.879	0.625	0.184	0.037	0.000	0.000

SU YILI (2006) YILLIK TOPLAM AKIM 5.94 MİLYON M3 46 MM. 1.5 LT/SN/Km2

15. Kizilirmak Havzasi

D15A152 ARASÖZÜ ÇOĞUN BARAJI GİRİŞ

YERİ : KIRŞEHİR-ANKARA YOLUNUN 22.KM SİNDEN SAĞA AYRILAN KARAHIDIRKÖYÜ YOLUNUN 3.KM SİNDEKİ KÖPRÜNÜN 3 KM MENBAINDADIR
34°2'50" Doğu - 39°21'15" Kuzey

YAĞIŞ ALANI : 213,64 km2 **YAKLAŞIK KOT** : 1106 m

GÖZLEM SÜRESİ : 14.10.1970 - 30.09.2006

ORTALAMA AKIMLAR : Gözlem süresinde 0.468 m3/sn. (30 Yıllık) 2006 Su yılında 0.198 m3/sn.

ANLIK EN ÇOK VE EN AZ AKIMLAR:

2006 Su yılında anlık ençok akım	:	1.35	m3/sn	13.02.2006
2006 Su yılında anlık enaz akım	:	0.003	m3/sn	01.08.2006
Gözlem süresinde anlık ençok akım	:	16.0	m3/sn	19.05.1976
Gözlem süresinde anlık enaz akım	:	0.000	m3/sn	03.08.1973

8. Anahtar Eğrisi (Seviyeler cm olarak)

Seviye	Akım	Seviye	Akım	Seviye	Akım	Seviye	Akım
1	0.000	11	0.150	36	1.1	61	2.3
3	0.001	16	0.340	41	1.4	71	2.8
5	0.018	21	0.520	46	1.6	81	3.3
7	0.055	26	0.700	51	1.8	91	3.8
8	0.075	31	0.920	56	2.1	101	4.3

Akımlar 01 Ekim 2005 'den 30 Eylül 2006' a kadar m3/sn olarak

Gün	Ekim	Kasım	Aralık	Ocak	Şubat	Mart	Nisan	Mayıs	Haziran	Temmuz	Ağustos	Eylül
01	0.044	0.130	0.158	0.185	0.158	0.660	0.500	0.340	0.130	0.062	0.003	0.018
02	0.044	0.130	0.158	0.185	0.158	0.660	0.500	0.340	0.130	0.062	0.003	0.018
03	0.044	0.130	0.158	0.185	0.130	0.620	0.309	0.309	0.107	0.062	0.003	0.018
04	0.044	0.130	0.158	0.185	0.158	0.620	0.309	0.309	0.107	0.062	0.003	0.018
05	0.044	0.130	0.158	0.185	0.107	0.620	0.309	0.309	0.083	0.062	0.003	0.018
06	0.062	0.130	0.158	0.216	0.130	0.620	0.309	0.309	0.062	0.062	0.003	0.018
07	0.062	0.130	0.158	0.216	0.247	0.620	0.309	0.309	0.062	0.062	0.003	0.018
08	0.062	0.130	0.158	0.216	0.309	0.620	0.309	0.309	0.062	0.062	0.003	0.018
09	0.062	0.130	0.158	0.216	0.309	0.620	0.309	0.309	0.062	0.062	0.003	0.018
10	0.062	0.130	0.158	0.185	0.278	0.580	0.309	0.309	0.062	0.062	0.003	0.018
11	0.062	0.130	0.158	0.185	0.628	0.580	0.309	0.309	0.062	0.062	0.003	0.018
12	0.062	0.130	0.158	0.185	1.11	0.580	0.309	0.309	0.062	0.062	0.003	0.018
13	0.076	0.130	0.158	0.185	1.06	0.580	0.278	0.309	0.062	0.062	0.003	0.018
14	0.076	0.130	0.158	0.185	0.884	0.580	0.278	0.278	0.062	0.062	0.003	0.018
15	0.076	0.130	0.158	0.185	0.838	0.580	0.278	0.278	0.062	0.062	0.003	0.018
16	0.076	0.130	0.185	0.185	0.792	0.540	0.278	0.278	0.062	0.062	0.003	0.018
17	0.100	0.130	0.185	0.185	0.974	0.540	0.278	0.278	0.062	0.062	0.003	0.018
18	0.100	0.130	0.158	0.158	0.746	0.540	0.278	0.247	0.062	0.062	0.003	0.018
19	0.100	0.130	0.158	0.158	0.884	0.500	0.278	0.247	0.062	0.062	0.003	0.018
20	0.100	0.170	0.185	0.185	0.838	0.500	0.278	0.216	0.062	0.062	0.003	0.018
21	0.100	0.247	0.158	0.185	0.792	0.500	0.278	0.185	0.062	0.062	0.003	0.018
22	0.100	0.216	0.158	0.158	0.660	0.500	0.278	0.158	0.062	0.062	0.003	0.018
23	0.100	0.216	0.185	0.185	0.620	0.500	0.278	0.158	0.062	0.062	0.003	0.018
24	0.100	0.185	0.158	0.158	0.620	0.500	0.278	0.158	0.062	0.062	0.003	0.018
25	0.100	0.158	0.158	0.158	0.620	0.500	0.278	0.158	0.062	0.062	0.003	0.018
26	0.100	0.158	0.158	0.158	0.660	0.500	0.278	0.130	0.062	0.062	0.003	0.018
27	0.130	0.158	0.185	0.158	0.660	0.500	0.278	0.130	0.062	0.062	0.003	0.018
28	0.130	0.158	0.185	0.158	0.660	0.500	0.278	0.130	0.062	0.062	0.003	0.018
29	0.130	0.158	0.185	0.158	-----	0.500	0.278	0.130	0.062	0.062	0.003	0.018
30	0.130	0.158	0.185	0.158	-----	0.500	0.278	0.130	0.062	0.062	0.003	0.018
31	0.130	-----	0.185	0.158	-----	0.500	-----	0.130	-----	0.062	0.003	-----
Maks.	0.130	0.340	0.216	0.216	1.35	0.660	0.500	0.340	0.130	0.062	0.003	0.018
Min.	0.044	0.130	0.107	0.158	0.015	0.500	0.278	0.130	0.062	0.062	0.003	0.018
Ortalama	0.084	0.148	0.166	0.179	0.572	0.557	0.303	0.242	0.070	0.062	0.003	0.018
LT/SN/Km2	0.394	0.695	0.776	0.840	2.68	2.61	1.42	1.13	0.329	0.290	0.014	0.084
AKIM mm.	1.05	1.80	2.08	2.25	6.48	6.98	3.68	3.03	0.852	0.777	0.038	0.218
MİL. M3	0.225	0.385	0.444	0.481	1.38	1.49	0.786	0.648	0.182	0.166	0.008	0.047

SU YILI (2006) YILLIK TOPLAM AKIM 6.24 MİLYON M3 29 MM. 0.9 LT/SN/Km2

15. Kizilirmak Havzasi

D15A153 YESİLHISAR DERESİ AKKÖY

YERİ : **YEŞİLHİSAR-AKKÖY BARAJI YOLU ÜZERİNDE VE BARAJ AKSINA 1KM MESAFEDEDİR.**
35°2'3" Doğu - 38°20'12" Kuzey

YAĞIŞ ALANI : **723,40 km2** **YAKLAŞIK KOT : 1198 m**

GÖZLEM SÜRESİ : **19.10.1970 - 30.09.2006**

ORTALAMA AKIMLAR : **Gözlem süresinde 0.446 m3/sn. (32 Yıllık) 2006 Su yılında 0.114 m3/sn.**

ANLIK EN ÇOK VE EN AZ AKIMLAR:

2006 Su yılında anlık ençok akım	**:**	**0.920**	**m3/sn**	**13.06.2006**
2006 Su yılında anlık enaz akım	**:**	**0.000**	**m3/sn**	**25.10.2005**
Gözlem süresinde anlık ençok akım	**:**	**42.0**	**m3/sn**	**05.06.1979**
Gözlem süresinde anlık enaz akım	**:**	**0.000**	**m3/sn**	**30.09.1974**

İstasyon için kullanılmış anahtar bulunamadı.

Akımlar 01 Ekim 2005 'den 30 Eylül 2006' a kadar m3/sn olarak

Gün	Ekim	Kasım	Aralık	Ocak	Şubat	Mart	Nisan	Mayıs	Haziran	Temmuz	Ağustos	Eylül
01	0.017	0.011	0.008	0.008	0.008	0.008	0.130	0.022	0.048	0.235	0.500	0.004
02	0.017	0.011	0.008	0.008	0.008	0.040	0.130	0.022	0.048	0.188	0.308	0.004
03	0.017	0.011	0.008	0.008	0.008	0.315	0.130	0.022	0.048	0.285	0.255	0.004
04	0.030	0.008	0.008	0.008	0.008	0.370	0.130	0.022	0.048	0.340	0.255	0.004
05	0.030	0.008	0.008	0.008	0.008	0.370	0.034	0.022	0.285	0.340	0.255	0.004
06	0.030	0.008	0.008	0.008	0.008	0.370	0.022	0.022	0.535	0.285	0.255	0.004
07	0.017	0.004	0.008	0.008	0.008	0.370	0.022	0.022	0.605	0.235	0.255	0.004
08	0.017	0.004	0.008	0.008	0.008	0.370	0.022	0.022	0.605	0.235	0.255	0.004
09	0.017	0.004	0.008	0.008	0.008	0.435	0.022	0.022	0.605	0.235	0.255	0.004
10	0.017	0.004	0.008	0.008	0.008	0.370	0.022	0.022	0.605	0.285	0.255	0.004
11	0.017	0.004	0.008	0.008	0.008	0.370	0.022	0.022	0.605	0.285	0.255	0.004
12	0.017	0.004	0.008	0.008	0.008	0.370	0.022	0.022	0.605	0.285	0.255	0.004
13	0.017	0.004	0.008	0.008	0.008	0.285	0.022	0.022	0.605	0.340	0.255	0.004
14	0.017	0.004	0.008	0.008	0.008	0.285	0.022	0.022	0.605	0.340	0.255	0.004
15	0.017	0.004	0.008	0.008	0.008	0.285	0.022	0.022	0.535	0.340	0.027	0.004
16	0.017	0.004	0.008	0.008	0.008	0.165	0.022	0.022	0.605	0.340	0.008	0.004
17	0.017	0.004	0.008	0.008	0.008	0.130	0.022	0.022	0.605	0.340	0.008	0.004
18	0.017	0.004	0.008	0.008	0.008	0.130	0.022	0.022	0.605	0.340	0.008	0.004
19	0.019	0.008	0.008	0.008	0.008	0.130	0.022	0.022	0.605	0.570	0.004	0.004
20	0.019	0.008	0.008	0.008	0.008	0.130	0.022	0.022	0.605	0.500	0.004	0.004
21	0.019	0.008	0.008	0.008	0.008	0.130	0.022	0.022	0.605	0.500	0.004	0.004
22	0.019	0.008	0.008	0.008	0.008	0.130	0.022	0.022	0.605	0.570	0.004	0.004
23	0.019	0.008	0.008	0.008	0.008	0.130	0.022	0.022	0.605	0.570	0.004	0.004
24	0.019	0.008	0.008	0.008	0.008	0.130	0.022	0.022	0.605	0.570	0.004	0.004
25	0.011	0.008	0.008	0.008	0.008	0.130	0.022	0.022	0.675	0.570	0.004	0.004
26	0.011	0.008	0.008	0.008	0.008	0.130	0.022	0.022	0.675	0.570	0.004	0.004
27	0.011	0.008	0.008	0.008	0.008	0.130	0.022	0.007	0.675	0.570	0.004	0.004
28	0.011	0.008	0.008	0.008	0.008	0.130	0.022	0.007	0.465	0.570	0.004	0.004
29	0.011	0.008	0.008	0.008	-----	0.130	0.022	0.007	0.148	0.570	0.004	0.004
30	0.011	0.008	0.008	0.008	-----	0.130	0.022	0.007	0.535	0.570	0.004	0.004
31	0.011	-----	0.008	0.008	-----	0.130	-----	0.007	-----	0.570	0.004	-----
Maks.	0.048	0.030	0.016	0.008	0.008	0.640	0.130	0.027	0.920	0.710	0.570	0.004
Min.	KURU	0.004	0.002	0.008	0.008	0.008	0.027	0.007	0.048	0.165	0.004	0.004
Ortalama	0.017	0.007	0.008	0.008	0.008	0.217	0.037	0.020	0.500	0.405	0.128	0.004
LT/SN/Km2	0.024	0.009	0.011	0.011	0.011	0.300	0.051	0.027	0.691	0.559	0.177	0.006
AKIM mm.	0.064	0.024	0.030	0.030	0.027	0.804	0.132	0.072	1.79	1.50	0.474	0.014
MİL. M3	0.046	0.017	0.021	0.021	0.019	0.581	0.095	0.052	1.30	1.08	0.343	0.010

SU YILI (2006) YILLIK TOPLAM AKIM 3.58 MİLYON M3 5 MM. 0.2 LT/SN/Km2

15. Kizilirmak Havzasi

D15A164 KIZILIRMAK NEHİRİ HÜSEYİNLİ

YERİ : ANKARA-ÇANKIRI YOLUNUN 110. KM SİNDE KIZILIRMAK İSTİKAMETİNE DÖNÜLÜR. 34 KM GİDİLDİĞİNDE İLÇE GİRİŞİNDEKİ KIZILIRMAK İLÇESİNDEDİR.
33°59'0" Doğu - 40°21'8" Kuzey

YAĞIŞ ALANI : 33422.00 km2 **YAKLAŞIK KOT** : 548 m

GÖZLEM SÜRESİ : 05.12.1968 - 30.09.2006

ORTALAMA AKIMLAR : Gözlem süresinde 27.613 m3/sn. (2 Yıllık) 2006 Su yılında 32.359 m3/sn.

ANLIK EN ÇOK VE EN AZ AKIMLAR:

2006 Su yılında anlık ençok akım	:	120.	m3/sn	04.02.2006
2006 Su yılında anlık enaz akım	:	10.0	m3/sn	20.12.2005
Gözlem süresinde anlık ençok akım	:	120.	m3/sn	04.02.2006
Gözlem süresinde anlık enaz akım	:	4.30	m3/sn	30.01.2005

İstasyon için kullanılmış anahtar bulunamadı.

Akımlar 01 Ekim 2005 'den 30 Eylül 2006' a kadar m3/sn olarak

Gün	Ekim	Kasım	Aralık	Ocak	Şubat	Mart	Nisan	Mayıs	Haziran	Temmuz	Ağustos	Eylül
01	18.1	15.6	14.0	11.6	107.	48.2	31.9	10.8	49.3	52.4	41.9	29.9
02	14.8	14.8	14.8	11.6	102.	58.8	26.2	10.8	51.4	51.4	38.8	31.9
03	14.0	13.2	17.3	11.6	104.	58.8	24.4	11.6	55.6	46.1	38.8	29.9
04	14.0	14.0	18.9	24.4	119.	58.8	23.5	13.2	62.1	47.2	21.6	29.9
05	15.6	15.6	18.1	33.8	106.	57.7	21.6	14.0	61.0	45.1	21.6	30.9
06	14.0	14.8	14.8	22.5	86.5	55.6	22.5	36.7	48.2	45.1	34.8	29.9
07	14.0	13.2	14.0	14.8	80.3	54.6	23.5	63.2	13.2	44.0	34.8	31.9
08	13.2	13.2	14.0	14.0	81.4	52.4	19.8	69.9	14.8	44.0	19.8	32.9
09	13.2	13.2	14.0	12.4	78.0	51.4	18.1	69.9	15.6	44.0	33.8	33.8
10	13.2	13.2	14.0	11.6	73.4	49.3	18.1	68.8	18.1	44.0	35.8	35.8
11	13.2	13.2	15.6	11.6	67.7	48.2	17.3	49.3	18.1	41.9	34.8	35.8
12	13.2	13.2	14.8	11.6	63.2	46.1	17.3	55.6	21.6	44.0	36.7	36.7
13	13.2	13.2	16.4	11.6	59.9	45.1	16.4	44.0	18.1	41.9	35.8	38.8
14	14.8	13.2	14.8	11.6	57.7	44.0	16.4	37.7	16.4	41.9	35.8	39.8
15	14.8	13.2	16.4	11.6	54.6	41.9	15.6	31.9	15.6	41.9	34.8	40.9
16	14.8	13.2	18.1	11.6	52.4	37.7	14.8	41.9	54.6	41.9	34.8	43.0
17	15.6	13.2	16.4	11.6	51.4	34.8	14.8	39.8	54.6	41.9	36.7	43.0
18	14.0	14.0	14.0	12.4	51.4	32.9	14.0	28.0	54.6	40.9	43.0	48.2
19	13.2	15.6	12.4	12.4	50.3	29.9	14.0	44.0	54.6	39.8	38.8	48.2
20	13.2	17.3	10.0	14.8	48.2	29.0	12.4	45.1	54.6	39.8	34.8	47.2
21	13.2	21.6	18.9	12.4	49.3	28.0	11.6	45.1	54.6	38.8	30.9	49.3
22	13.2	23.5	15.6	12.4	49.3	27.1	10.8	44.0	56.7	38.8	31.9	49.3
23	13.2	21.6	12.4	11.6	49.3	27.1	18.1	46.1	51.4	43.0	43.0	51.4
24	13.2	16.4	12.4	11.6	46.1	26.2	14.8	45.1	49.3	43.0	41.9	51.4
25	13.2	15.6	12.4	18.9	45.1	25.3	12.4	45.1	50.3	39.8	32.9	52.4
26	13.2	14.8	12.4	28.0	43.0	25.3	11.6	47.2	50.3	39.8	30.9	51.4
27	13.2	13.2	12.4	31.9	43.0	23.5	10.8	48.2	49.3	40.9	30.9	41.9
28	13.2	13.2	12.4	54.6	43.0	28.0	10.8	51.4	48.2	41.9	29.9	28.0
29	13.2	13.2	12.4	86.5	-----	35.8	10.8	49.3	49.3	40.9	29.0	24.4
30	13.2	13.2	11.6	101.	-----	47.2	10.8	48.2	51.4	39.8	29.0	18.9
31	13.2	-----	11.6	87.8	-----	47.2	-----	49.3	-----	40.9	29.0	-----
Maks.	26.2	26.2	23.5	114.	120.	69.9	37.7	87.8	69.9	53.5	46.1	56.7
Min.	13.2	12.4	10.0	10.8	43.0	21.6	10.0	10.8	13.2	37.7	14.8	16.4
Ortalama	13.8	14.9	14.4	24.1	66.5	41.2	16.8	42.1	42.1	42.8	33.8	38.6
LT/SN/Km2	0.414	0.445	0.432	0.720	1.99	1.23	0.504	1.26	1.26	1.28	1.01	1.15
AKIM mm.	1.11	1.15	1.16	1.93	4.81	3.30	1.31	3.37	3.26	3.43	2.71	2.99
MİL. M3	37.1	38.6	38.6	64.4	161.	110.	43.6	113.	109.	115.	90.5	99.9

SU YILI (2006) YILLIK TOPLAM AKIM 1020.70 MİLYON M3 31 MM. 1.0 LT/SN/Km2

15. Kizilirmak Havzasi

D15A167 SARMİSAKLI SUYU SARIMSAKLI BARAJI GİRIŞI

YERİ : **KAYSERİ-BÜNYAN KARAYOLUNUN 35.KM SİNDEN SOLA DÖNÜLÜR.1 KM MESAFEDE KÖPRÜNÜN MEMBAINDADIR**

35°46'42" Doğu - 38°52'16" Kuzey

YAĞIŞ ALANI : **398,80 km2** **YAKLAŞIK KOT : 1202 m**

GÖZLEM SÜRESİ : **01.10.1973 - 30.09.2006**

ORTALAMA AKIMLAR : **Gözlem süresinde 1.686 m3/sn. (30 Yıllık) 2006 Su yılında 1.452 m3/sn.**

ANLIK EN ÇOK VE EN AZ AKIMLAR:

2006 Su yılında anlık ençok akım	**:**	**2.46**	**m3/sn**	**26.04.2006**
2006 Su yılında anlık enaz akım	**:**	**0.408**	**m3/sn**	**26.07.2006**
Gözlem süresinde anlık ençok akım	**:**	**17.0**	**m3/sn**	**16.12.1981**
Gözlem süresinde anlık enaz akım	**:**	**0.165**	**m3/sn**	**29.06.1985**

İstasyon için kullanılmış anahtar bulunamadı.

Akımlar 01 Ekim 2005 'den 30 Eylül 2006' a kadar m3/sn olarak

Gün	Ekim	Kasım	Aralık	Ocak	Şubat	Mart	Nisan	Mayıs	Haziran	Temmuz	Ağustos	Eylül
01	1.75	1.75	1.75	1.75	1.99	2.06	1.60	1.68	1.15	0.837	0.560	0.720
02	1.75	1.75	1.75	1.91	2.06	1.99	1.68	2.06	1.08	0.837	0.611	0.720
03	1.75	1.75	1.75	2.06	2.06	1.83	1.68	1.91	1.08	0.778	0.720	0.720
04	1.75	1.75	1.75	2.06	2.06	1.75	1.68	1.83	1.02	0.778	0.611	0.720
05	1.75	1.75	1.75	2.06	2.06	1.75	1.68	1.75	1.02	0.778	0.560	0.778
06	1.68	1.68	1.68	1.99	2.06	1.68	1.75	1.75	0.837	0.953	0.510	0.837
07	1.75	1.75	1.75	2.06	2.14	1.68	1.75	1.60	1.02	0.953	0.560	0.837
08	1.75	1.75	1.75	2.06	2.14	1.60	1.68	1.60	0.837	0.953	0.560	0.837
09	1.75	1.75	1.75	2.06	2.14	1.75	1.60	1.60	0.837	0.837	0.611	0.895
10	1.75	1.75	1.75	2.06	2.14	1.68	1.60	1.68	0.837	1.02	0.611	0.837
11	1.75	1.75	1.75	2.06	2.14	1.68	1.68	1.68	0.837	0.953	0.611	0.895
12	1.75	1.75	1.75	2.06	2.14	1.68	1.68	1.60	0.837	0.837	0.611	0.953
13	1.75	1.75	1.68	2.06	2.14	1.60	1.60	1.60	0.778	0.778	0.611	0.953
14	1.68	1.75	1.68	2.06	2.06	1.60	1.60	1.68	0.778	0.720	0.560	1.02
15	1.68	1.75	1.68	2.06	2.06	1.68	1.60	1.60	0.778	0.720	0.611	1.08
16	1.68	1.68	1.68	2.06	2.06	1.60	1.68	1.60	0.778	0.720	0.611	1.08
17	1.75	1.75	1.68	2.06	2.06	1.68	1.60	1.68	0.662	0.720	0.611	1.08
18	1.75	1.75	1.75	2.06	2.06	1.68	1.68	1.60	0.662	0.720	0.611	1.02
19	1.75	1.75	1.68	2.06	1.91	1.75	1.60	1.60	0.662	0.662	0.611	1.08
20	1.75	1.75	1.75	2.06	1.99	1.68	1.60	1.60	0.662	0.662	0.611	1.15
21	1.68	1.68	1.68	2.06	2.06	1.60	1.60	1.60	0.662	0.611	0.611	1.21
22	1.68	1.75	1.75	2.06	2.06	1.75	1.54	1.54	0.611	0.611	0.611	1.28
23	1.68	1.75	1.75	2.06	2.06	1.68	1.60	1.41	0.662	0.611	0.611	1.41
24	1.75	1.75	1.75	2.06	2.06	1.68	1.83	1.34	0.560	0.611	0.611	1.41
25	1.75	1.75	1.75	2.06	2.06	1.68	1.99	1.34	0.611	0.611	0.611	1.47
26	1.75	1.68	1.68	2.06	2.06	1.75	1.75	1.41	0.611	0.611	0.611	1.41
27	1.75	1.68	1.75	1.91	2.06	1.68	1.75	1.34	0.611	0.611	0.662	1.41
28	1.75	1.68	1.75	2.06	2.06	1.68	1.75	1.41	0.720	0.611	0.611	1.41
29	1.75	1.68	1.75	2.06	-----	1.68	1.75	1.28	0.837	0.560	0.611	1.41
30	1.75	1.68	1.75	1.99	-----	1.60	1.75	1.28	0.837	0.560	0.611	1.47
31	1.75	-----	1.75	2.06	-----	1.68	-----	1.21	-----	0.611	0.720	-----
Maks.	1.91	1.91	1.91	2.14	2.22	2.22	2.46	2.29	1.41	1.28	1.15	1.47
Min.	1.68	1.68	1.68	1.75	1.68	1.34	1.41	0.953	0.510	0.408	0.459	0.662
Ortalama	1.73	1.73	1.73	2.04	2.07	1.71	1.68	1.58	0.796	0.737	0.608	1.07
LT/SN/Km2	4.35	4.34	4.34	5.10	5.19	4.28	4.21	3.95	2.00	1.85	1.53	2.68
AKIM mm.	11.6	11.3	11.6	13.7	12.6	11.5	10.9	10.6	5.17	4.95	4.08	6.95
MİL. M3	4.64	4.49	4.63	5.45	5.01	4.57	4.35	4.22	2.06	1.97	1.63	2.77

SU YILI (2006) YILLIK TOPLAM AKIM 45.79 MİLYON M3 115 MM. 3.6 LT/SN/Km2

15. Kizilirmak Havzasi

D15A168 HASBEK SUYU HASBEK

YERİ : SARIKAYA İLÇESİNE 23 KM MESAFEDEKİ HASBEK BUCAĞI KÖPRÜSÜNDEDİR.
35°32'44" Doğu - 39°32'39" Kuzey

YAĞIŞ ALANI : 160,90 km2 YAKLAŞIK KOT : 1122 m

GÖZLEM SÜRESİ : 24.11.1972 - 30.09.2006

ORTALAMA AKIMLAR : Gözlem süresinde 0.608 m3/sn. (30 Yıllık) 2006 Su yılında 0.129 m3/sn.

ANLIK EN ÇOK VE EN AZ AKIMLAR:

2006 Su yılında anlık ençok akım	:	0.750	m3/sn	02.05.2006
2006 Su yılında anlık enaz akım	:	0.000	m3/sn	22.08.2006
Gözlem süresinde anlık ençok akım	:	34.0	m3/sn	22.08.2002
Gözlem süresinde anlık enaz akım	:	0.000	m3/sn	10.08.2001

3. Anahtar Eğrisi (Seviyeler cm olarak)

Seviye	Akım	Seviye	Akım	Seviye	Akım	Seviye	Akım
1	0.000	11	0.160	25	1.1	90	9.7
3	0.004	13	0.250	35	2.0	110	12.7
5	0.018	15	0.350	45	3.2	180	45.5
7	0.048	17	0.470	55	4.6	200	66.7
9	0.094	19	0.600	70	6.7	220	96.7

Akımlar 01 Ekim 2005 'den 30 Eylül 2006' a kadar m3/sn olarak

Gün	Ekim	Kasım	Aralık	Ocak	Şubat	Mart	Nisan	Mayıs	Haziran	Temmuz	Ağustos	Eylül
01	0.018	0.070	0.125	0.125	0.125	0.250	0.205	0.410	0.125	0.009	0.004	KURU
02	0.018	0.070	0.125	0.125	0.125	0.250	0.470	0.470	0.125	0.009	0.004	KURU
03	0.018	0.070	0.125	0.125	0.125	0.250	0.530	0.530	0.125	0.009	0.004	KURU
04	0.018	0.070	0.125	0.125	0.094	0.250	0.410	0.470	0.125	0.009	0.004	KURU
05	0.018	0.070	0.125	0.125	0.070	0.250	0.350	0.410	0.125	0.009	0.004	KURU
06	0.018	0.094	0.125	0.125	0.030	0.250	0.300	0.350	0.125	0.009	0.004	KURU
07	0.018	0.125	0.125	0.160	0.048	0.250	0.250	0.350	0.125	0.009	0.004	KURU
08	0.018	0.125	0.125	0.160	0.125	0.250	0.250	0.350	0.125	0.009	0.004	KURU
09	0.018	0.125	0.125	0.160	0.250	0.250	0.250	0.410	0.125	0.009	0.004	KURU
10	0.018	0.125	0.125	0.160	0.160	0.250	0.250	0.350	0.125	0.009	0.004	KURU
11	0.018	0.125	0.125	0.160	0.205	0.250	0.250	0.350	0.125	0.009	0.004	KURU
12	0.018	0.125	0.125	0.160	0.470	0.250	0.250	0.350	0.125	0.009	0.004	KURU
13	0.018	0.125	0.125	0.160	0.410	0.205	0.250	0.350	0.125	0.009	0.004	KURU
14	0.018	0.125	0.125	0.160	0.350	0.250	0.250	0.350	0.094	0.009	0.004	KURU
15	0.018	0.125	0.125	0.160	0.300	0.250	0.250	0.350	0.094	0.009	0.004	KURU
16	0.018	0.125	0.125	0.125	0.250	0.160	0.250	0.350	0.094	0.009	0.004	KURU
17	0.018	0.125	0.125	0.125	0.250	0.160	0.205	0.350	0.094	0.009	0.004	KURU
18	0.018	0.125	0.125	0.125	0.250	0.160	0.205	0.350	0.094	0.004	0.004	KURU
19	0.018	0.125	0.125	0.125	0.250	0.160	0.205	0.300	0.094	0.004	0.004	KURU
20	0.018	0.125	0.125	0.125	0.350	0.205	0.205	0.300	0.094	0.004	0.004	KURU
21	0.018	0.125	0.125	0.125	0.350	0.205	0.205	0.300	0.094	0.004	0.004	KURU
22	0.018	0.125	0.125	0.125	0.300	0.250	0.205	0.300	0.094	0.004	0.004	KURU
23	0.018	0.125	0.125	0.125	0.300	0.250	0.205	0.300	0.094	0.004	KURU	KURU
24	0.030	0.125	0.125	0.125	0.300	0.250	0.205	0.160	0.094	0.004	KURU	KURU
25	0.070	0.125	0.125	0.125	0.250	0.250	0.250	0.125	0.094	0.004	KURU	KURU
26	0.070	0.125	0.094	0.125	0.250	0.250	0.300	0.125	0.094	0.004	KURU	KURU
27	0.070	0.125	0.094	0.125	0.250	0.250	0.250	0.410	0.094	0.004	KURU	KURU
28	0.070	0.125	0.094	0.125	0.250	0.250	0.250	0.160	0.018	0.004	KURU	KURU
29	0.070	0.125	0.125	0.125	-----	0.250	0.250	0.125	0.009	0.004	KURU	KURU
30	0.070	0.125	0.125	0.125	-----	0.250	0.410	0.125	0.009	0.004	KURU	KURU
31	0.070	-----	0.125	0.125	-----	0.205	-----	0.125	-----	0.004	KURU	-----
Maks.	0.094	0.205	0.125	0.205	0.600	0.530	0.670	0.750	0.125	0.009	0.004	KURU
Min.	0.018	0.070	0.030	0.125	0.030	0.004	0.125	0.094	0.004	0.004	KURU	KURU
Ortalama	0.030	0.115	0.122	0.135	0.232	0.233	0.271	0.315	0.099	0.007	0.003	KURU
LT/SN/Km2	0.187	0.713	0.758	0.840	1.44	1.45	1.68	1.96	0.617	0.042	0.018	0.000
AKIM mm.	0.502	1.85	2.03	2.25	3.48	3.87	4.36	5.24	1.60	0.112	0.047	0.000
MİL. M3	0.081	0.298	0.327	0.362	0.560	0.623	0.701	0.843	0.257	0.018	0.008	0.000

SU YILI (2006) YILLIK TOPLAM AKIM 4.08 MİLYON M3 25 MM. 0.8 LT/SN/Km2

15. Kizilirmak Havzasi

D15A172 Sarmisakli S. Ambar Reg.

YERİ : **1978KAYSERİ ANKARA KARAYOLUNDA ANBAR BÖLGE TRAFİK DENETLEMEBİNASI ARKASINDAKİ YOLA GİRİLİR.1200M İLERİDE İLK KÖPRÜDEDİR.**
35°21'59" Doğu - 38°45'58" Kuzey

YAĞIŞ ALANI : **1360,00 km2** **YAKLAŞIK KOT : 965 m**

GÖZLEM SÜRESİ : **04.07.1975 - 30.09.2006**

ORTALAMA AKIMLAR : **Gözlem süresinde 2.053 m3/sn. (22 Yıllık) 2006 Su yılında 0.783 m3/sn.**

ANLIK EN ÇOK VE EN AZ AKIMLAR:

2006 Su yılında anlık ençok akım	**:**	**3.60**	**m3/sn**	**03.02.2006**
2006 Su yılında anlık enaz akım	**:**	**0.000**	**m3/sn**	**01.07.2006**
Gözlem süresinde anlık ençok akım	**:**	**28.7**	**m3/sn**	**29.07.2001**
Gözlem süresinde anlık enaz akım	**:**	**0.000**	**m3/sn**	**26.06.2003**

İstasyon için kullanılmış anahtar bulunamadı.

Akımlar 01 Ekim 2005 'den 30 Eylül 2006' a kadar m3/sn olarak

Gün	Ekim	Kasım	Aralık	Ocak	Şubat	Mart	Nisan	Mayıs	Haziran	Temmuz	Ağustos	Eylül
01	0.130	0.100	0.380	0.380	2.88	3.60	2.40	0.460	0.042	KURU	KURU	KURU
02	0.130	0.130	0.380	0.380	3.36	3.60	2.20	0.460	0.042	KURU	KURU	0.032
03	0.130	0.130	0.380	0.380	3.60	3.60	2.00	0.460	0.042	KURU	KURU	0.032
04	0.130	0.130	0.380	0.380	3.60	3.36	1.80	0.460	0.032	KURU	KURU	0.042
05	0.130	0.130	0.380	0.380	3.60	3.36	1.60	0.460	0.032	KURU	KURU	0.042
06	0.130	0.130	0.380	0.380	3.60	3.36	1.40	0.460	0.013	KURU	KURU	0.042
07	0.130	0.130	0.380	0.380	3.60	3.36	1.26	0.460	0.013	KURU	KURU	0.042
08	0.130	0.130	0.380	0.380	3.60	3.36	1.12	0.460	0.023	KURU	KURU	0.060
09	0.130	0.130	0.380	0.380	3.60	3.36	0.980	0.540	0.023	KURU	KURU	0.060
10	0.130	0.130	0.380	0.380	3.60	3.36	0.840	0.540	0.032	KURU	KURU	0.060
11	0.080	0.130	0.380	0.380	3.60	3.36	0.700	0.540	0.032	KURU	KURU	0.060
12	0.080	0.130	0.380	0.380	3.60	3.36	0.620	0.540	0.042	KURU	KURU	0.060
13	0.080	0.130	0.380	0.380	3.60	3.36	0.540	0.460	0.042	KURU	KURU	0.080
14	0.100	0.130	0.380	0.380	3.60	3.36	0.460	0.460	0.060	KURU	KURU	0.100
15	0.100	0.130	0.380	0.380	3.60	3.12	0.460	0.380	0.060	KURU	KURU	0.100
16	0.130	0.130	0.380	0.460	3.60	3.12	0.460	0.380	0.060	KURU	KURU	0.130
17	0.130	0.130	0.380	0.540	3.60	2.88	0.460	0.300	0.060	KURU	KURU	0.130
18	0.130	0.130	0.380	0.620	3.60	2.88	0.460	0.250	0.060	KURU	KURU	0.160
19	0.130	0.130	0.380	0.700	3.60	2.40	0.460	0.200	0.060	KURU	KURU	0.160
20	0.130	0.130	0.380	0.840	3.60	2.40	0.460	0.200	0.060	KURU	KURU	0.200
21	0.130	0.160	0.380	0.980	3.60	2.40	0.460	0.200	0.060	KURU	KURU	0.200
22	0.130	0.200	0.380	1.12	3.60	2.40	0.460	0.160	0.060	KURU	KURU	0.200
23	0.130	0.250	0.380	1.40	3.60	2.40	0.460	0.130	0.042	KURU	KURU	0.200
24	0.130	0.300	0.380	1.80	3.60	2.40	0.460	0.130	0.042	KURU	KURU	0.200
25	0.130	0.380	0.380	2.20	3.60	2.40	0.460	0.100	0.042	KURU	KURU	0.200
26	0.130	0.460	0.380	2.40	3.60	2.40	0.460	0.080	0.042	KURU	KURU	0.200
27	0.130	0.540	0.380	2.88	3.60	2.40	0.460	0.080	0.042	KURU	KURU	0.200
28	0.130	0.620	0.380	2.88	3.60	2.40	0.460	0.080	0.042	KURU	KURU	0.200
29	0.100	0.540	0.380	2.88	-----	2.40	0.460	0.060	0.042	KURU	KURU	0.200
30	0.100	0.460	0.380	2.88	-----	2.40	0.460	0.042	0.042	KURU	KURU	0.200
31	0.100	-----	0.380	2.88	-----	2.40	-----	0.042	-----	KURU	KURU	-----
Maks.	0.130	0.620	0.380	2.88	3.60	3.60	2.40	0.540	0.060	KURU	KURU	0.200
Min.	0.080	0.100	0.380	0.380	2.88	2.40	0.460	0.042	0.013	KURU	KURU	KURU
Ortalama	0.120	0.216	0.380	1.07	3.57	2.93	0.843	0.309	0.043	KURU	KURU	0.120
LT/SN/Km2	0.088	0.159	0.279	0.787	2.62	2.16	0.620	0.227	0.032	0.000	0.000	0.088
AKIM mm.	0.237	0.412	0.748	2.11	6.34	5.78	1.61	0.608	0.082	0.000	0.000	0.228
MİL. M3	0.322	0.560	1.02	2.87	8.63	7.86	2.18	0.827	0.111	0.000	0.000	0.310

SU YILI (2006) YILLIK TOPLAM AKIM 24.69 MİLYON M3 18 MM. 0.6 LT/SN/Km2

15. Kizilirmak Havzasi

D15A177 TERME ÇAYI KOYUNBABA

YERİ : **ANKARA-ŞABANÖZÜ YOLUNUN 60 KM.SİNDEN SAĞA DÖNÜLEREK 15 KM. SONRA KOYUNBABA KÖYÜNE GİDİLİR.İSTASYON KOYUNBABA KÖYÜNÜN 5 KM. ALTINDADIR.**
33°19'0" Doğu - 40°20'0" Kuzey

YAĞIŞ ALANI : **754.00 km2** **YAKLAŞIK KOT : 778 m**

GÖZLEM SÜRESİ : **16.10.1977 - 30.09.2006**

ORTALAMA AKIMLAR : **Gözlem süresinde 1.800 m3/sn. (27 Yıllık) 2006 Su yılında 1.474 m3/sn.**

ANLIK EN ÇOK VE EN AZ AKIMLAR:

2006 Su yılında anlık ençok akım	:	**58.6**	**m3/sn**	**03.03.2006**
2006 Su yılında anlık enaz akım	:	**0.008**	**m3/sn**	**03.10.2005**
Gözlem süresinde anlık ençok akım	:	**135.**	**m3/sn**	**28.12.2001**
Gözlem süresinde anlık enaz akım	:	**0.000**	**m3/sn**	**05.09.1994**

İstasyon için kullanılmış anahtar bulunamadı.

Akımlar 01 Ekim 2005 'den 30 Eylül 2006' a kadar m3/sn olarak

Gün	Ekim	Kasım	Aralık	Ocak	Şubat	Mart	Nisan	Mayıs	Haziran	Temmuz	Ağustos	Eylül
01	0.036	0.190	0.265	0.265	0.265	13.6	5.56	1.97	0.145	0.340	0.058	0.036
02	0.014	0.190	0.265	0.340	0.340	15.9	4.80	1.97	0.145	0.190	0.058	0.036
03	0.008	0.190	0.265	0.340	0.340	36.2	4.80	1.97	0.145	0.190	0.058	0.036
04	0.008	0.190	0.265	0.340	0.340	16.9	4.49	1.97	0.100	0.190	0.058	0.058
05	0.008	0.340	0.265	0.340	0.340	12.2	4.49	1.97	0.079	0.145	0.058	0.058
06	0.008	0.265	0.265	0.340	0.340	12.7	4.17	1.48	0.058	0.145	0.058	0.036
07	0.008	0.265	0.265	0.340	0.340	13.6	3.54	1.48	0.058	0.145	0.058	0.036
08	0.008	0.265	0.265	0.340	0.340	14.5	3.54	1.48	0.058	0.100	0.058	0.036
09	0.008	0.265	0.265	0.340	0.340	15.9	3.54	1.48	0.079	0.100	0.058	0.036
10	0.008	0.265	0.265	0.340	0.340	9.95	3.54	1.48	0.079	0.100	0.036	0.036
11	0.008	0.265	0.265	0.340	0.340	8.22	3.54	1.48	0.100	0.145	0.058	0.036
12	0.008	0.265	0.265	0.340	0.340	7.46	2.91	1.48	0.100	0.145	0.036	0.036
13	0.008	0.265	0.265	0.340	0.340	8.60	2.28	1.48	0.079	0.079	0.058	0.036
14	0.008	0.265	0.265	0.340	0.340	12.2	2.28	1.48	0.079	0.079	0.058	0.036
15	0.008	0.265	0.265	0.340	0.340	12.2	2.28	1.48	0.058	0.079	0.079	0.036
16	0.008	0.265	0.265	0.340	0.340	9.95	2.28	1.32	0.058	0.079	0.079	0.036
17	0.014	0.265	0.265	0.340	0.340	9.05	2.28	1.32	0.058	0.058	0.058	0.036
18	0.036	0.265	0.265	0.340	0.340	7.84	2.28	1.32	0.058	0.058	0.058	0.036
19	0.036	0.265	0.265	0.340	0.340	7.84	2.28	1.15	0.058	0.058	0.058	0.036
20	0.036	0.265	0.265	0.340	0.340	7.08	2.28	0.817	0.058	0.058	0.058	0.036
21	0.036	0.265	0.265	0.340	0.340	7.08	2.28	0.817	0.058	0.058	0.058	0.036
22	0.036	0.265	0.265	0.340	0.340	7.46	2.28	0.265	0.058	0.058	0.058	0.058
23	0.036	0.265	0.265	0.340	0.983	10.4	2.28	0.190	0.058	0.058	0.079	0.058
24	0.079	0.265	0.265	0.340	1.65	12.7	2.28	0.190	0.079	0.058	0.079	0.058
25	0.145	0.265	0.265	0.340	2.91	10.9	1.97	0.190	0.079	0.058	0.079	0.036
26	0.145	0.265	0.265	0.340	7.46	8.22	1.97	0.145	0.079	0.058	0.079	0.036
27	0.190	0.265	0.265	0.340	10.4	7.46	1.97	0.145	0.079	0.058	0.036	0.036
28	0.190	0.265	0.265	0.340	7.84	6.70	1.97	0.145	0.079	0.058	0.014	0.100
29	0.190	0.265	0.265	0.340	-----	6.32	1.97	0.145	0.100	0.058	0.036	0.100
30	0.190	0.265	0.265	0.340	-----	5.94	1.97	0.145	0.495	0.058	0.036	0.100
31	0.190	-----	0.265	0.265	-----	5.94	-----	0.145	-----	0.058	0.036	-----
Maks.	0.190	0.340	0.265	0.340	15.5	58.6	5.56	1.97	0.817	0.495	0.079	0.145
Min.	0.008	0.190	0.265	0.265	0.265	5.56	1.97	0.145	0.058	0.036	0.008	0.036
Ortalama	0.055	0.257	0.265	0.335	1.38	11.0	2.94	1.07	0.094	0.101	0.056	0.046
LT/SN/Km2	0.073	0.342	0.351	0.445	1.83	14.6	3.89	1.42	0.124	0.134	0.075	0.061
AKIM mm.	0.196	0.885	0.941	1.19	4.43	39.1	10.1	3.79	0.323	0.358	0.200	0.158
MİL. M3	0.148	0.667	0.710	0.898	3.34	29.5	7.61	2.86	0.243	0.270	0.151	0.119

SU YILI (2006) YILLIK TOPLAM AKIM 46.52 MİLYON M3 62 MM. 2.0 LT/SN/Km2

15. Kizilirmak Havzasi

D15A180 KIZILIRMAK OĞLAKPINAR

YERİ : **SİVAS - ŞARKIŞLA İLÇESI BOZKURT KÖYÜ GIRIŞINDEKI KÖPRÜDEDIR.**
36°22'32" Doğu - 39°29'37" Kuzey

YAĞIŞ ALANI : **11073,60 km2** **YAKLAŞIK KOT : 1188 m**

GÖZLEM SÜRESİ : **15.11.1977 - 30.09.2006**

ORTALAMA AKIMLAR : **Gözlem süresinde 49.642 m3/sn. (27 Yıllık) 2006 Su yılında 45.419 m3/sn.**

ANLIK EN ÇOK VE EN AZ AKIMLAR:

2006 Su yılında anlık ençok akım	**:**	**338.**	**m3/sn**	**27.03.2006**
2006 Su yılında anlık enaz akım	**:**	**5.90**	**m3/sn**	**29.07.2006**
Gözlem süresinde anlık ençok akım	**:**	**792.**	**m3/sn**	**15.05.1998**
Gözlem süresinde anlık enaz akım	**:**	**0.000**	**m3/sn**	**01.09.1982**

Akımlar 01 Ekim 2005 'den 30 Eylül 2006' a kadar m3/sn olarak

Gün	Ekim	Kasım	Aralık	Ocak	Şubat	Mart	Nisan	Mayıs	Haziran	Temmuz	Ağustos	Eylül
01	9.62	16.8	19.6	19.0	19.6	41.1	141.	121.	65.2	23.2	9.20	7.22
02	9.62	16.8	19.6	19.6	19.6	48.3	127.	131.	60.9	23.2	8.21	7.22
03	10.0	17.9	19.6	19.6	19.6	59.9	129.	127.	56.7	20.8	7.88	7.22
04	10.9	18.4	19.6	20.2	19.6	69.6	122.	165.	53.6	19.6	8.21	7.22
05	11.3	19.6	19.6	20.2	22.6	92.0	121.	125.	50.4	19.0	7.88	7.22
06	11.3	21.4	19.6	20.2	24.4	86.0	143.	114.	48.3	18.4	7.55	7.22
07	11.3	23.2	18.4	20.8	16.8	84.8	125.	106.	45.2	18.4	7.22	7.22
08	11.3	22.6	18.4	21.4	19.0	94.4	133.	135.	44.1	19.0	7.22	7.22
09	10.9	21.4	18.4	21.4	20.8	133.	161.	177.	43.1	19.6	7.22	7.22
10	10.9	20.8	18.4	21.4	22.6	171.	213.	213.	40.2	18.4	7.22	7.22
11	10.9	20.2	18.4	20.8	23.2	133.	201.	179.	36.6	17.3	7.22	7.22
12	10.9	19.6	19.0	20.2	23.8	107.	199.	155.	33.0	16.8	7.22	7.22
13	10.9	19.0	19.0	20.2	27.4	93.2	173.	139.	33.0	16.2	7.22	7.22
14	10.9	19.0	19.6	20.2	29.8	88.4	167.	131.	33.0	15.6	7.22	7.22
15	10.9	18.4	19.6	19.6	29.8	94.4	175.	127.	31.4	15.6	7.22	7.22
16	10.9	18.4	19.6	19.0	28.2	111.	185.	117.	30.6	14.5	7.22	7.22
17	11.3	18.4	19.0	18.4	27.4	118.	193.	115.	29.0	14.0	7.22	7.22
18	12.1	17.9	19.6	17.9	25.0	106.	145.	137.	28.2	13.4	7.22	7.22
19	15.1	17.9	19.6	17.9	22.0	99.3	125.	122.	27.4	13.4	7.22	7.22
20	17.9	18.4	19.6	17.9	23.8	95.6	115.	111.	25.8	12.6	7.22	7.22
21	20.2	18.4	20.8	18.4	25.8	90.8	107.	103.	24.4	12.1	7.22	7.22
22	21.4	19.0	25.0	18.4	25.0	87.2	107.	96.8	23.8	12.6	7.22	7.22
23	20.2	19.0	25.0	18.4	23.8	87.2	103.	92.0	22.6	12.1	7.22	7.22
24	19.6	20.2	23.8	18.4	23.8	89.6	106.	87.2	21.4	12.1	7.22	7.22
25	19.0	20.2	23.2	18.4	23.8	101.	159.	82.4	20.8	11.7	7.22	7.22
26	18.4	20.2	22.6	19.0	25.0	201.	213.	78.8	20.2	11.3	7.22	7.22
27	17.9	19.6	22.0	19.6	28.2	303.	169.	78.8	19.0	11.3	7.22	7.22
28	17.3	19.6	21.4	19.6	34.8	215.	139.	81.2	19.0	11.3	7.22	7.22
29	17.3	19.6	20.8	19.6	-----	181.	122.	81.2	20.2	10.9	7.22	7.22
30	16.8	19.6	19.6	19.6	-----	163.	122.	74.0	23.2	9.20	7.22	7.22
31	16.8	-----	19.0	19.6	-----	149.	-----	69.6	-----	9.20	7.22	-----
Maks.	22.0	24.4	25.8	21.4	38.4	338.	317.	233.	68.5	23.8	9.20	8.21
Min.	9.62	16.8	18.4	17.3	10.0	38.4	99.3	67.4	18.4	5.90	7.22	7.22
Ortalama	14.0	19.4	20.2	19.5	24.1	116.	148.	118.	34.3	15.3	7.40	7.22
LT/SN/Km2	1.26	1.75	1.83	1.76	2.18	10.5	13.4	10.7	3.10	1.38	0.668	0.652
AKIM mm.	3.38	4.54	4.90	4.72	5.27	28.0	34.6	28.7	8.04	3.69	1.79	1.69
MİL. M3	37.5	50.2	54.2	52.3	58.3	311.	384.	317.	89.0	40.8	19.8	18.7

SU YILI (2006) YILLIK TOPLAM AKIM 1432.80 MİLYON M3 129 MM. 4.1 LT/SN/Km2

15. Kizilirmak Havzasi

D15A182 BOZKIR BARAJI GİRIS

YERİ : **KIRŞEHİR-KESİK KÖPRÜ-ORTAKÖY-GÖKLER YOLUNUN 1.KM SİNDE BULU-NAN KÖPRÜNÜN MANSABINDADIR**

34°4'1" Doğu - 38°45'32" Kuzey

YAĞIŞ ALANI : **73,00 km2** **YAKLAŞIK KOT : 1142 m**

GÖZLEM SÜRESİ : **01.10.1977 - 30.09.2006**

ORTALAMA AKIMLAR : **Gözlem süresinde 0.215 m3/sn. (28 Yıllık) 2006 Su yılında 0.014 m3/sn.**

ANLIK EN ÇOK VE EN AZ AKIMLAR:

2006 Su yılında anlık ençok akım	**:**	**0.920**	**m3/sn**	**24.04.2006**
2006 Su yılında anlık enaz akım	**:**	**0.000**	**m3/sn**	**16.06.2006**
Gözlem süresinde anlık ençok akım	**:**	**20.5**	**m3/sn**	**19.05.2004**
Gözlem süresinde anlık enaz akım	**:**	**0.000**	**m3/sn**	**03.11.1978**

İstasyon için kullanılmış anahtar bulunamadı.

Akımlar 01 Ekim 2005 'den 30 Eylül 2006' a kadar m3/sn olarak

Gün	Ekim	Kasım	Aralık	Ocak	Şubat	Mart	Nisan	Mayıs	Haziran	Temmuz	Ağustos	Eylül
01	0.013	0.004	0.059	0.016	0.016	0.016	0.016	0.016	0.016	KURU	KURU	KURU
02	0.013	0.004	0.059	0.016	0.016	0.016	0.016	0.092	0.016	KURU	KURU	KURU
03	0.013	0.004	0.059	0.016	0.016	0.016	0.016	0.059	0.016	KURU	KURU	KURU
04	0.013	0.004	0.059	0.016	0.016	0.016	0.016	0.034	0.016	KURU	KURU	KURU
05	0.006	0.004	0.059	0.016	0.016	0.016	0.007	0.034	0.016	KURU	KURU	KURU
06	0.006	0.004	0.059	0.007	0.016	0.016	0.007	0.016	0.016	KURU	KURU	KURU
07	0.006	0.004	0.059	0.007	0.016	0.007	0.007	0.016	0.016	KURU	KURU	KURU
08	0.006	0.004	0.059	0.007	0.016	0.004	0.007	0.016	0.016	KURU	KURU	KURU
09	0.006	0.004	0.059	0.007	0.016	0.004	0.007	0.016	0.016	KURU	KURU	0.002
10	0.006	0.002	0.059	0.007	0.016	0.007	0.007	0.016	0.016	KURU	KURU	0.006
11	0.006	0.004	0.059	0.007	0.016	0.016	0.007	0.016	0.007	KURU	KURU	0.006
12	0.006	0.016	0.059	0.007	0.016	0.016	0.007	0.016	0.002	KURU	KURU	0.006
13	0.006	0.016	0.034	0.007	0.016	0.016	0.007	0.016	0.001	KURU	KURU	0.006
14	0.006	0.016	0.034	0.007	0.016	0.016	0.007	0.016	KURU	KURU	KURU	0.006
15	0.006	0.016	0.034	0.007	0.016	0.016	0.007	0.016	KURU	KURU	KURU	0.006
16	0.006	0.034	0.016	0.007	0.016	0.016	0.007	0.016	KURU	KURU	KURU	0.006
17	0.013	0.034	0.016	0.007	0.016	0.016	0.007	0.016	KURU	KURU	KURU	0.006
18	0.023	0.034	0.016	0.007	0.016	0.016	0.007	0.016	KURU	KURU	KURU	0.006
19	0.023	0.034	0.016	0.007	0.034	0.016	0.007	0.016	KURU	KURU	KURU	0.006
20	0.013	0.034	0.016	0.007	0.034	0.016	0.007	0.016	KURU	KURU	KURU	0.006
21	0.013	0.059	0.016	0.007	0.059	0.016	0.007	0.016	KURU	KURU	KURU	0.006
22	0.004	0.059	0.016	0.007	0.034	0.016	0.007	0.016	KURU	KURU	KURU	0.006
23	0.004	0.059	0.016	0.007	0.016	0.016	0.007	0.016	KURU	KURU	KURU	0.006
24	0.004	0.059	0.016	0.007	0.016	0.016	0.231	0.016	KURU	KURU	KURU	0.006
25	0.004	0.059	0.016	0.007	0.016	0.016	0.059	0.016	KURU	KURU	KURU	0.006
26	0.004	0.059	0.016	0.007	0.016	0.016	0.034	0.016	KURU	KURU	KURU	0.006
27	0.004	0.059	0.016	0.007	0.016	0.016	0.034	0.016	KURU	KURU	KURU	0.006
28	0.004	0.059	0.016	0.016	0.016	0.016	0.034	0.016	KURU	KURU	KURU	0.006
29	0.004	0.059	0.016	0.016	-----	0.016	0.034	0.016	KURU	KURU	KURU	0.006
30	0.004	0.059	0.016	0.016	-----	0.016	0.016	0.016	KURU	KURU	KURU	0.006
31	0.004	-----	0.016	0.016	-----	0.016	-----	0.016	-----	KURU	KURU	-----
Maks.	0.023	0.092	0.092	0.016	0.059	0.092	0.920	0.177	0.016	KURU	KURU	0.006
Min.	0.004	0.002	0.016	0.007	0.016	0.004	0.007	0.016	KURU	KURU	KURU	KURU
Ortalama	0.008	0.029	0.034	0.010	0.019	0.015	0.021	0.021	0.006	KURU	KURU	0.004
LT/SN/Km2	0.110	0.395	0.471	0.132	0.267	0.201	0.292	0.288	0.078	0.000	0.000	0.058
AKIM mm.	0.295	1.02	1.26	0.353	0.645	0.537	0.756	0.770	0.201	0.000	0.000	0.151
MİL. M3	0.022	0.075	0.092	0.026	0.047	0.039	0.055	0.056	0.015	0.000	0.000	0.011

SU YILI (2006) YILLIK TOPLAM AKIM 0.44 MİLYON M3 6 MM. 0.2 LT/SN/Km2

15. Kizilirmak Havzasi

D15A185 YILDIZIRMAĞI ZENGİ

YERİ : **SİVAS MERKEZ ZENGİ KÖYÜ GİRİŞİ KÖPRÜSÜNDEDİR**
36°51'23" Doğu - 39°57'23" Kuzey

YAĞIŞ ALANI : **1035,00 km2** **YAKLAŞIK KOT : 1308 m**

GÖZLEM SÜRESİ : **03.07.1979 - 30.09.2006**

ORTALAMA AKIMLAR : **Gözlem süresinde 10.681 m3/sn. (23 Yıllık) 2006 Su yılında 7.946 m3/sn.**

ANLIK EN ÇOK VE EN AZ AKIMLAR:

2006 Su yılında anlık ençok akım	:	**89.5**	**m3/sn**	**26.03.2006**
2006 Su yılında anlık enaz akım	:	**2.10**	**m3/sn**	**25.09.2006**
Gözlem süresinde anlık ençok akım	:	**225.**	**m3/sn**	**05.03.2004**
Gözlem süresinde anlık enaz akım	:	**0.006**	**m3/sn**	**24.09.1983**

Akımlar 01 Ekim 2005 'den 30 Eylül 2006' a kadar m3/sn olarak

Gün	Ekim	Kasım	Aralık	Ocak	Şubat	Mart	Nisan	Mayıs	Haziran	Temmuz	Ağustos	Eylül
01	2.95	3.15	4.70	3.55	3.55	17.2	26.0	16.0	8.22	3.78	3.15	2.55
02	3.35	3.35	4.70	3.55	3.55	20.5	33.5	16.4	7.64	3.78	3.15	2.55
03	3.15	3.35	4.47	3.55	3.55	24.0	34.0	16.4	7.35	3.78	3.15	2.55
04	3.15	3.35	4.47	3.55	3.55	35.0	29.0	14.5	7.06	3.78	3.15	2.75
05	2.95	3.55	4.47	3.55	3.55	24.5	26.0	16.0	6.48	4.01	2.95	2.75
06	2.95	3.55	4.24	3.78	3.55	28.0	23.5	17.6	6.19	4.01	2.75	2.55
07	2.75	3.55	4.01	4.24	3.78	33.0	22.0	18.8	6.19	4.01	2.75	2.55
08	2.75	3.55	3.78	4.24	4.70	52.0	22.0	22.0	5.90	4.01	2.75	2.55
09	2.75	3.78	3.78	4.01	5.42	47.2	24.0	18.0	5.66	3.78	2.55	2.55
10	2.75	3.78	3.78	4.01	5.18	31.5	25.5	16.4	5.42	3.78	2.75	2.55
11	2.75	3.55	3.78	4.01	5.18	23.0	28.0	14.9	5.42	3.78	2.75	2.40
12	2.75	3.55	3.78	4.01	7.64	18.8	24.0	13.7	5.42	3.78	2.75	2.40
13	2.75	3.55	3.78	4.01	8.22	18.0	20.5	13.3	5.42	3.55	2.75	2.40
14	2.75	3.35	3.55	3.78	7.64	19.6	18.8	13.3	5.18	3.55	2.55	2.55
15	2.95	3.35	3.55	3.55	7.06	21.5	18.0	12.2	4.94	3.55	2.55	2.55
16	3.15	3.35	3.55	3.35	6.19	19.2	19.2	11.5	4.94	3.55	2.55	2.55
17	3.15	3.55	3.55	3.35	5.66	18.4	16.8	19.6	4.70	3.55	2.55	2.55
18	3.15	3.55	3.55	3.35	5.90	17.6	14.9	17.6	4.70	3.55	2.55	2.55
19	4.01	3.55	3.78	3.55	5.66	17.2	14.1	15.2	4.47	3.55	2.55	2.40
20	3.55	3.55	3.78	3.35	5.66	16.4	13.7	13.7	4.47	3.55	2.55	2.40
21	3.78	3.78	3.78	3.55	5.66	15.2	13.0	12.6	4.24	3.35	2.75	2.40
22	3.55	4.47	3.78	3.55	5.66	16.8	12.2	11.9	4.01	3.35	2.75	2.95
23	3.55	4.47	3.78	3.55	5.66	17.2	11.9	11.2	4.01	3.55	2.55	2.75
24	3.55	4.24	3.55	3.55	5.90	19.2	11.5	10.2	4.01	3.55	2.55	2.75
25	3.35	4.47	3.55	3.55	6.48	48.4	12.6	9.82	4.01	3.55	2.75	2.55
26	3.35	4.47	3.55	3.55	7.93	68.5	12.2	9.14	3.78	3.55	2.75	2.10
27	3.35	4.47	3.55	3.55	10.8	46.6	11.2	11.2	3.78	3.35	2.55	2.10
28	3.35	4.70	3.55	3.35	12.6	36.5	11.2	11.9	3.78	3.15	2.55	2.10
29	3.35	4.70	3.55	3.35	-----	30.5	11.2	10.2	3.78	3.15	2.55	2.10
30	3.35	4.94	3.55	3.55	-----	27.5	15.2	9.14	3.78	3.15	2.55	2.10
31	3.35	-----	3.55	3.55	-----	27.0	-----	8.51	-----	3.15	2.75	-----
Maks.	4.94	4.94	5.18	4.24	16.4	89.5	36.5	28.0	8.22	4.24	3.15	5.18
Min.	2.40	3.15	3.55	3.15	3.35	14.9	10.8	8.22	3.78	3.15	2.40	2.10
Ortalama	3.17	3.82	3.83	3.64	5.92	27.6	19.2	14.0	5.17	3.60	2.72	2.48
LT/SN/Km2	3.06	3.69	3.70	3.52	5.72	26.7	18.5	13.5	4.99	3.48	2.63	2.40
AKIM mm.	8.21	9.56	9.92	9.43	13.8	71.5	48.1	36.1	12.9	9.31	7.03	6.22
MİL. M3	8.50	9.90	10.3	9.76	14.3	74.0	49.7	37.4	13.4	9.64	7.28	6.44

SU YILI (2006) YILLIK TOPLAM AKIM 250.62 MİLYON M3 242 MM. 7.7 LT/SN/Km2

15. Kizilirmak Havzasi

D15A195 BALABAN ÇAYI KUŞÇUALİ

YERİ : **ANKARA ELMADAĞ İLÇESİNDEN SAĞA DÖNÜLÜR, 10 KM SONRA KUŞCUALİ KÖYÜNÜN 1 KM MANSABINDADIR**

33°15'0" Doğu - 39°47'0" Kuzey

YAĞIŞ ALANI : **997.00 km2** **YAKLAŞIK KOT : 850 m**

GÖZLEM SÜRESİ : **04.09.1981 - 30.09.2006**

ORTALAMA AKIMLAR : **Gözlem süresinde 1.093 m3/sn. (15 Yıllık) 2006 Su yılında 0.444 m3/sn.**

ANLIK EN ÇOK VE EN AZ AKIMLAR:

2006 Su yılında anlık ençok akım	:	**6.70**	**m3/sn**	**29.06.2006**
2006 Su yılında anlık enaz akım	:	**0.038**	**m3/sn**	**08.08.2006**
Gözlem süresinde anlık ençok akım	:	**56.0**	**m3/sn**	**28.06.1992**
Gözlem süresinde anlık enaz akım	:	**0.000**	**m3/sn**	**08.10.1989**

12. Anahtar Eğrisi (Seviyeler cm olarak)

Seviye	Akım	Seviye	Akım	Seviye	Akım	Seviye	Akım
20	0.008	30	0.064	70	1.6	120	4.7
22	0.013	40	0.341	80	2.1	130	5.4
24	0.020	50	0.688	90	2.6	140	6.2
26	0.029	55	0.884	100	3.3	150	7.1
28	0.044	60	1.1	110	4.0	160	8.0

Akımlar 01 Ekim 2005 'den 30 Eylül 2006' a kadar m3/sn olarak

Gün	Ekim	Kasım	Aralık	Ocak	Şubat	Mart	Nisan	Mayıs	Haziran	Temmuz	Ağustos	Eylül
01	0.110	0.140	0.192	0.192	0.214	2.50	0.560	0.598	0.236	0.750	0.066	0.038
02	0.110	0.140	0.192	0.236	0.214	2.66	0.560	0.636	0.280	0.496	0.066	0.085
03	0.236	0.140	0.192	0.214	0.258	3.38	0.528	0.750	0.258	0.280	0.066	0.056
04	0.140	0.258	0.328	0.258	0.258	3.38	0.432	0.674	0.236	0.170	0.066	0.066
05	0.125	0.328	0.258	0.236	0.258	2.98	0.432	0.636	0.192	0.140	0.075	0.075
06	0.125	0.258	0.214	0.214	0.258	2.82	0.432	0.598	0.236	0.125	0.075	0.075
07	0.125	0.214	0.192	0.214	0.258	2.66	0.432	0.598	0.192	0.110	0.056	0.066
08	0.125	0.192	0.192	0.214	0.258	2.58	0.432	0.560	0.170	0.110	0.038	0.066
09	0.125	0.192	0.192	0.214	0.258	2.66	0.432	0.496	0.170	0.110	0.038	0.066
10	0.125	0.192	0.192	0.214	0.258	2.01	0.432	0.400	0.170	0.110	0.038	0.056
11	0.125	0.192	0.192	0.214	0.258	1.80	0.432	0.352	0.095	0.110	0.038	0.066
12	0.125	0.192	0.192	0.214	0.496	1.74	0.432	0.328	0.110	0.095	0.038	0.075
13	0.125	0.192	0.192	0.214	0.598	1.80	0.432	0.328	0.110	0.095	0.038	0.075
14	0.125	0.192	0.192	0.192	0.636	2.29	0.432	0.304	0.125	0.095	0.038	0.075
15	0.258	0.192	0.192	0.192	0.636	2.01	0.432	0.304	0.125	0.095	0.038	0.066
16	0.214	0.192	0.192	0.192	0.674	1.74	0.432	0.280	0.125	0.095	0.038	0.075
17	0.258	0.192	0.192	0.192	0.598	1.74	0.432	0.280	0.125	0.095	0.038	0.075
18	0.085	0.352	0.192	0.192	0.496	1.68	0.432	0.304	0.110	0.095	0.038	0.075
19	0.110	0.328	0.192	0.192	0.560	2.08	0.432	0.304	0.110	0.095	0.038	0.075
20	0.155	0.280	0.192	0.214	0.712	2.01	0.400	0.236	0.095	0.085	0.038	0.085
21	0.170	0.258	0.192	0.214	1.20	2.01	0.376	0.214	0.304	0.110	0.038	0.110
22	0.170	0.192	0.192	0.214	1.74	2.01	0.400	0.192	3.54	0.110	0.046	0.192
23	0.170	0.192	0.192	0.304	2.08	2.08	0.560	0.192	1.15	0.170	0.038	0.214
24	0.170	0.192	0.192	0.280	2.29	2.08	0.496	0.214	0.674	0.155	0.038	0.214
25	0.170	0.192	0.192	0.352	2.50	1.87	0.464	0.192	0.636	0.140	0.038	0.214
26	0.170	0.192	0.192	0.328	2.66	1.87	0.432	0.192	0.598	0.110	0.038	0.214
27	0.192	0.214	0.192	0.304	3.06	1.68	0.432	0.236	0.560	0.110	0.038	0.214
28	0.170	0.214	0.192	0.236	2.66	1.50	0.400	0.258	0.528	0.085	0.046	0.192
29	0.155	0.192	0.192	0.214	-----	1.20	0.400	0.258	0.214	0.085	0.046	0.192
30	0.140	0.192	0.192	0.214	-----	0.960	0.464	0.236	1.32	0.075	0.038	0.170
31	0.140	-----	0.192	0.214	-----	0.750	-----	0.236	-----	0.075	0.038	-----
Maks.	3.62	0.750	0.464	0.432	3.30	3.38	0.560	0.792	6.70	0.876	0.095	0.236
Min.	0.056	0.140	0.155	0.192	0.192	0.750	0.376	0.155	0.085	0.066	0.038	0.038
Ortalama	0.153	0.213	0.199	0.229	0.941	2.08	0.446	0.367	0.426	0.148	0.045	0.111
LT/SN/Km2	0.153	0.214	0.200	0.229	0.944	2.09	0.447	0.368	0.428	0.148	0.045	0.111
AKIM mm.	0.411	0.554	0.535	0.614	2.28	5.59	1.16	0.987	1.11	0.397	0.122	0.287
MİL. M3	0.410	0.552	0.534	0.612	2.28	5.58	1.16	0.984	1.11	0.396	0.121	0.287

SU YILI (2006) YILLIK TOPLAM AKIM 14.03 MİLYON M3 14 MM. 0.4 LT/SN/Km2

15. Kizilirmak Havzasi

D15A206 ARSIZÖZÜ UZUNLU BRAJI

YERİ : BOĞAZLIYAN-ÇAYIRALAN YOLUNUN 30.KM SİNDEN SAĞA DÖNÜLEREK DERE YATAĞINDAKİ İSTASYONA VARILIR.
35°28'3" Doğu - 39°13'47" Kuzey

YAĞIŞ ALANI : 574,80 km2 **YAKLAŞIK KOT** : 1188 m

GÖZLEM SÜRESİ : 03.09.1984 - 30.09.2006

ORTALAMA AKIMLAR : Gözlem süresinde 1.196 m3/sn. (21 Yıllık) 2006 Su yılında 0.368 m3/sn.

ANLIK EN ÇOK VE EN AZ AKIMLAR:

2006 Su yılında anlık ençok akım	:	1.65	m3/sn	29.06.2006
2006 Su yılında anlık enaz akım	:	0.000	m3/sn	25.08.2006
Gözlem süresinde anlık ençok akım	:	84.0	m3/sn	17.05.1990
Gözlem süresinde anlık enaz akım	:	0.000	m3/sn	17.07.1994

38. Anahtar Eğrisi (Seviyeler cm olarak)

Seviye	Akım	Seviye	Akım	Seviye	Akım	Seviye	Akım
1	0.001	51	5.8	101	19.4	153	39.9
11	0.356	61	8.0	112	23.1	166	45.6
21	1.2	71	10.5	122	26.7	179	51.9
31	2.4	82	13.3	131	30.6	194	59.1
41	4.0	91	16.3	142	34.8		

Akımlar 01 Ekim 2005 'den 30 Eylül 2006' a kadar m3/sn olarak

Gün	Ekim	Kasım	Aralık	Ocak	Şubat	Mart	Nisan	Mayıs	Haziran	Temmuz	Ağustos	Eylül
01	0.123	0.400	0.400	0.470	0.470	0.620	0.900	0.800	0.540	0.220	0.010	KURU
02	0.123	0.400	0.340	0.470	0.540	0.620	0.900	0.900	0.470	0.055	0.010	0.002
03	0.123	0.400	0.400	0.470	0.540	0.540	0.900	0.900	0.400	0.055	0.010	KURU
04	0.123	0.400	0.400	0.470	0.470	0.540	0.800	0.900	0.400	0.055	0.010	KURU
05	0.123	0.340	0.340	0.400	0.540	0.620	0.800	0.800	0.400	0.055	0.010	0.002
06	0.123	0.400	0.340	0.470	0.620	0.620	0.720	0.800	0.270	0.055	0.002	KURU
07	0.123	0.400	0.400	0.470	0.620	0.620	0.800	0.720	0.220	0.055	0.010	KURU
08	0.170	0.340	0.400	0.470	0.620	0.620	0.900	0.720	0.170	0.055	0.010	KURU
09	0.170	0.340	0.400	0.470	0.620	0.620	0.800	0.720	0.170	0.055	0.002	KURU
10	0.170	0.340	0.400	0.470	0.620	0.620	0.800	0.720	0.055	0.055	0.002	KURU
11	0.170	0.340	0.400	0.400	0.540	0.540	0.800	0.720	0.055	0.055	0.010	KURU
12	0.170	0.340	0.400	0.470	0.620	0.620	0.720	0.720	0.055	0.055	0.010	0.002
13	0.170	0.340	0.400	0.470	0.540	0.620	0.720	0.720	0.055	0.055	0.010	KURU
14	0.170	0.340	0.400	0.400	0.620	0.620	0.800	0.720	0.055	0.055	0.002	0.002
15	0.220	0.400	0.400	0.400	0.620	0.720	0.800	0.720	0.055	0.029	0.010	KURU
16	0.220	0.400	0.400	0.400	0.620	0.720	0.900	0.800	0.055	0.010	0.010	0.002
17	0.170	0.340	0.400	0.470	0.620	0.620	0.800	0.800	0.055	0.010	0.010	KURU
18	0.220	0.400	0.400	0.470	0.620	0.620	0.720	0.720	0.055	0.010	0.010	0.002
19	0.270	0.400	0.400	0.400	0.620	0.720	0.720	0.720	0.055	0.010	0.002	KURU
20	0.270	0.400	0.400	0.400	0.620	0.620	0.720	0.720	0.055	0.010	0.002	KURU
21	0.270	0.400	0.340	0.470	0.620	0.540	0.720	0.720	0.055	0.002	0.010	KURU
22	0.340	0.340	0.340	0.470	0.620	0.720	0.800	0.720	0.055	0.002	0.010	0.002
23	0.270	0.340	0.400	0.470	0.620	0.800	0.800	0.720	0.055	0.010	0.010	KURU
24	0.270	0.340	0.400	0.400	0.620	0.800	0.900	0.620	0.055	0.010	0.002	0.002
25	0.270	0.340	0.400	0.400	0.540	0.720	0.900	0.540	0.055	0.010	KURU	0.002
26	0.340	0.340	0.400	0.470	0.620	0.800	0.900	0.540	0.055	0.002	KURU	0.002
27	0.340	0.340	0.470	0.470	0.540	0.800	0.900	0.620	0.055	0.010	KURU	0.002
28	0.340	0.400	0.470	0.400	0.620	0.720	0.800	0.620	0.055	0.010	KURU	KURU
29	0.340	0.340	0.470	0.470	-----	0.720	0.720	0.540	0.540	0.010	KURU	KURU
30	0.400	0.400	0.400	0.470	-----	0.900	0.720	0.540	0.470	0.010	KURU	0.002
31	0.400	-----	0.470	0.470	-----	0.900	-----	0.540	-----	0.002	KURU	-----
Maks.	0.400	0.400	0.470	0.470	0.620	0.900	0.900	0.900	1.65	0.270	0.010	0.002
Min.	0.090	0.270	0.340	0.400	0.470	0.540	0.720	0.540	0.055	0.002	KURU	KURU
Ortalama	0.226	0.368	0.399	0.447	0.589	0.674	0.806	0.712	0.170	0.035	0.006	0.001
LT/SN/Km2	0.393	0.640	0.695	0.778	1.03	1.17	1.40	1.24	0.295	0.061	0.010	0.001
AKIM mm.	1.05	1.66	1.86	2.08	2.48	3.14	3.63	3.32	0.766	0.164	0.028	0.004
MİL. M3	0.605	0.954	1.07	1.20	1.43	1.80	2.09	1.91	0.440	0.094	0.016	0.002

SU YILI (2006) YILLIK TOPLAM AKIM 11.61 MİLYON M3 20 MM. 0.6 LT/SN/Km2

15. Kizilirmak Havzasi

D15A216 KÖTÜ DERE BÜYÜK TAŞLIK

YERİ : 1986SORGUN YOZGAT YOLUNUN 12 KM SİNDEN SOLA DÖNÜLÜP TAŞLIK KÖYÜ-NE GİRİLİR.İSTASYON KÖYÜN 50 M KUZEYİNDEDİR.
35°2'6" Doğu - 39°48'13" Kuzey

YAĞIŞ ALANI : 51,70 km2 **YAKLAŞIK KOT :** 1120 m

GÖZLEM SÜRESİ : 06.05.1986 - 30.09.2006

ORTALAMA AKIMLAR : Gözlem süresinde 0.207 m3/sn. (16 Yıllık) 2006 Su yılında 0.079 m3/sn.

ANLIK EN ÇOK VE EN AZ AKIMLAR:

2006 Su yılında anlık ençok akım	:	1.54	m3/sn	03.03.2006
2006 Su yılında anlık enaz akım	:	0.000	m3/sn	01.10.2005
Gözlem süresinde anlık ençok akım	:	15.1	m3/sn	20.04.2002
Gözlem süresinde anlık enaz akım	:	0.000	m3/sn	23.12.1986

İstasyon için kullanılmış anahtar bulunamadı.

Akımlar 01 Ekim 2005 'den 30 Eylül 2006' a kadar m3/sn olarak

Gün	Ekim	Kasım	Aralık	Ocak	Şubat	Mart	Nisan	Mayıs	Haziran	Temmuz	Ağustos	Eylül
01	KURU	KURU	KURU	KURU	0.036	0.418	0.310	0.158	0.052	0.072	KURU	KURU
02	KURU	KURU	KURU	KURU	0.036	0.310	0.472	0.196	0.052	0.072	KURU	KURU
03	KURU	KURU	KURU	KURU	0.052	0.472	0.364	0.196	0.036	0.072	KURU	KURU
04	KURU	KURU	KURU	KURU	0.052	0.364	0.272	0.196	0.036	0.072	KURU	KURU
05	KURU	KURU	KURU	KURU	0.072	0.272	0.234	0.158	0.036	0.072	KURU	KURU
06	KURU	KURU	KURU	KURU	0.072	0.234	0.234	0.158	0.036	0.072	KURU	KURU
07	KURU	KURU	KURU	KURU	0.097	0.196	0.234	0.158	0.036	0.052	KURU	KURU
08	KURU	KURU	KURU	KURU	0.120	0.158	0.234	0.120	0.036	0.052	KURU	KURU
09	KURU	KURU	KURU	KURU	0.158	0.234	0.196	0.120	0.036	0.052	KURU	KURU
10	KURU	KURU	KURU	KURU	0.196	0.158	0.234	0.097	0.036	0.052	KURU	KURU
11	KURU	KURU	KURU	KURU	0.234	0.158	0.234	0.097	0.036	0.052	KURU	KURU
12	KURU	KURU	KURU	KURU	0.272	0.158	0.196	0.097	0.036	0.052	KURU	KURU
13	KURU	KURU	KURU	KURU	0.310	0.120	0.158	0.097	0.022	0.052	KURU	KURU
14	KURU	KURU	KURU	KURU	0.310	0.120	0.196	0.097	0.022	0.052	KURU	KURU
15	KURU	KURU	KURU	KURU	0.310	0.234	0.234	0.097	0.022	0.052	KURU	KURU
16	KURU	KURU	KURU	KURU	0.310	0.234	0.364	0.097	0.022	0.052	KURU	KURU
17	KURU	KURU	KURU	KURU	0.310	0.272	0.234	0.097	0.022	0.052	KURU	KURU
18	KURU	KURU	KURU	KURU	0.364	0.234	0.196	0.097	0.022	0.052	KURU	KURU
19	KURU	KURU	KURU	KURU	0.364	0.418	0.196	0.097	0.022	0.052	KURU	KURU
20	KURU	KURU	KURU	KURU	0.364	0.418	0.158	0.072	0.022	0.052	KURU	KURU
21	KURU	KURU	KURU	KURU	0.364	0.418	0.158	0.072	0.022	0.052	KURU	KURU
22	KURU	KURU	KURU	KURU	0.364	0.310	0.158	0.072	0.022	0.052	KURU	KURU
23	KURU	KURU	KURU	KURU	0.364	0.272	0.158	0.072	0.022	0.052	KURU	KURU
24	KURU	KURU	KURU	KURU	0.364	0.272	0.196	0.072	0.022	0.052	KURU	KURU
25	KURU	KURU	KURU	KURU	0.418	0.472	0.158	0.072	0.022	0.052	KURU	KURU
26	KURU	KURU	KURU	KURU	0.418	0.526	0.158	0.052	0.022	0.052	0.052	0.052
27	KURU	KURU	KURU	0.014	0.418	0.418	0.158	0.052	0.022	0.052	0.014	0.014
28	KURU	KURU	KURU	0.014	0.418	0.310	0.158	0.052	0.022	0.052	0.014	0.014
29	KURU	KURU	KURU	0.014	-----	0.272	0.158	0.052	0.052	0.052	KURU	KURU
30	KURU	KURU	KURU	0.014	-----	0.272	0.196	0.052	0.072	0.052	KURU	KURU
31	KURU	-----	KURU	0.022	-----	0.272	-----	0.052	-----	0.052	KURU	-----
Maks.	KURU	KURU	KURU	0.022	0.418	1.54	0.908	0.310	1.54	0.072	0.052	0.052
Min.	KURU	KURU	KURU	KURU	0.036	0.120	0.120	0.052	0.022	0.052	KURU	KURU
Ortalama	KURU	KURU	KURU	0.003	0.256	0.290	0.220	0.102	0.031	0.056	0.003	0.003
LT/SN/Km2	0.000	0.000	0.000	0.049	4.95	5.61	4.26	1.98	0.606	1.08	0.050	0.052
AKIM mm.	0.000	0.000	0.000	0.130	12.0	15.0	11.0	5.30	1.57	2.89	0.134	0.134
MİL. M3	0.000	0.000	0.000	0.007	0.619	0.777	0.571	0.274	0.081	0.150	0.007	0.007

SU YILI (2006) YILLIK TOPLAM AKIM 2.49 MİLYON M3 48 MM. 1.5 LT/SN/Km2

15. Kizilirmak Havzasi

D15A220 YAHYALI SUYU DERNAJ KANAL GİRIŞ

YERİ : **YAHYALI İLÇESİNİN İSMET MAHALLESİNDEKİ YAHYALI SUYU ÜZERİN-DEKİ REGÜLATÖRDEN AYRILAN DERİVASYON KANALI ÜZERİNDE REGÜLATÖRE 100M MESAFEDEDİR. 35°22'11" Doğu - 38°8'4" Kuzey**

YAĞIŞ ALANI : **0,00 km2** **YAKLAŞIK KOT : 1139 m**

GÖZLEM SÜRESİ : **22.01.1987 - 30.09.2006**

ORTALAMA AKIMLAR : **Gözlem süresinde 1.416 m3/sn. (17 Yıllık) 2006 Su yılında 0.598 m3/sn.**

ANLIK EN ÇOK VE EN AZ AKIMLAR:

2006 Su yılında anlık ençok akım	**:**	**4.70**	**m3/sn**	**10.04.2006**
2006 Su yılında anlık enaz akım	**:**	**0.000**	**m3/sn**	**01.10.2005**
Gözlem süresinde anlık ençok akım	**:**	**18.6**	**m3/sn**	**13.04.1992**
Gözlem süresinde anlık enaz akım	**:**	**0.000**	**m3/sn**	**01.10.1987**

İstasyon için kullanılmış anahtar bulunamadı.

Akımlar 01 Ekim 2005 'den 30 Eylül 2006' a kadar m3/sn olarak

Gün	Ekim	Kasım	Aralık	Ocak	Şubat	Mart	Nisan	Mayıs	Haziran	Temmuz	Ağustos	Eylül
01	KURU	0.022	0.380	0.210	0.165	0.240	2.30	3.40	1.25	KURU	KURU	KURU
02	KURU	0.090	0.380	0.190	0.165	0.350	2.50	3.92	1.35	KURU	KURU	KURU
03	KURU	0.090	0.380	0.190	0.165	0.480	2.50	3.60	1.35	KURU	KURU	KURU
04	KURU	0.090	0.380	0.190	0.165	0.660	2.70	3.60	1.35	KURU	KURU	KURU
05	KURU	0.190	0.380	0.190	0.165	0.660	2.50	3.76	0.960	KURU	KURU	KURU
06	KURU	0.190	0.380	0.190	0.165	0.660	2.30	3.50	0.008	KURU	KURU	KURU
07	KURU	0.190	0.380	0.190	0.165	0.660	2.30	3.20	KURU	KURU	KURU	KURU
08	KURU	0.190	0.320	0.190	0.165	0.660	2.60	3.00	KURU	KURU	KURU	KURU
09	KURU	0.240	0.320	0.190	0.165	0.660	2.70	3.00	KURU	KURU	KURU	KURU
10	KURU	0.240	0.320	0.190	0.165	0.660	3.92	2.70	KURU	KURU	KURU	KURU
11	KURU	0.240	0.320	0.190	0.165	0.660	4.40	2.30	KURU	KURU	KURU	KURU
12	KURU	0.320	0.320	0.190	0.210	0.660	3.50	2.20	KURU	KURU	KURU	KURU
13	KURU	0.320	0.320	0.190	0.210	0.660	3.60	2.10	KURU	KURU	KURU	KURU
14	KURU	0.320	0.320	0.190	0.210	0.660	3.60	2.10	KURU	KURU	KURU	KURU
15	KURU	0.320	0.320	0.190	0.210	0.660	3.60	2.00	KURU	KURU	KURU	KURU
16	KURU	0.320	0.260	0.165	0.210	0.660	3.60	1.90	KURU	KURU	KURU	KURU
17	KURU	0.320	0.260	0.165	0.210	0.660	3.50	1.90	KURU	KURU	KURU	KURU
18	KURU	0.320	0.260	0.165	0.210	0.700	2.90	1.80	KURU	KURU	KURU	KURU
19	KURU	0.320	0.260	0.165	0.210	0.780	2.80	1.80	KURU	KURU	KURU	KURU
20	KURU	0.320	0.260	0.165	0.210	0.700	2.80	1.70	KURU	KURU	KURU	KURU
21	KURU	0.320	0.260	0.165	0.210	0.780	2.50	1.60	KURU	KURU	KURU	KURU
22	KURU	0.320	0.260	0.165	0.210	0.860	2.50	1.50	KURU	KURU	KURU	KURU
23	KURU	0.320	0.210	0.165	0.210	2.00	2.30	1.40	KURU	KURU	KURU	KURU
24	KURU	0.320	0.210	0.165	0.210	2.20	2.30	1.40	KURU	KURU	KURU	KURU
25	KURU	0.320	0.210	0.165	0.210	2.20	2.30	1.25	KURU	KURU	KURU	KURU
26	KURU	0.380	0.210	0.165	0.210	2.10	2.30	0.900	KURU	KURU	KURU	KURU
27	KURU	0.380	0.210	0.165	0.210	1.95	2.30	0.860	KURU	KURU	KURU	KURU
28	KURU	0.380	0.210	0.165	0.210	1.80	2.30	0.860	KURU	KURU	KURU	KURU
29	KURU	0.380	0.210	0.165	-----	1.80	2.70	1.20	KURU	KURU	KURU	KURU
30	KURU	0.380	0.210	0.165	-----	1.95	2.70	1.35	KURU	KURU	KURU	KURU
31	KURU	-----	0.210	0.165	-----	1.95	-----	1.35	-----	KURU	KURU	-----
Maks.	KURU	0.380	0.380	0.210	0.210	2.30	4.70	4.40	1.35	KURU	KURU	KURU
Min.	KURU	KURU	0.210	0.165	0.165	0.210	2.30	0.820	KURU	KURU	KURU	KURU
Ortalama	KURU	0.272	0.288	0.178	0.192	1.03	2.83	2.17	0.209	KURU	KURU	KURU
LT/SN/Km2	0.000	0.000	0.000	0.000	0.000	0.000	0.000	0.000	0.000	0.000	0.000	0.000
AKIM mm.	0.000	0.000	0.000	0.000	0.000	0.000	0.000	0.000	0.000	0.000	0.000	0.000
MİL. M3	0.000	0.704	0.772	0.476	0.465	2.77	7.33	5.80	0.542	0.000	0.000	0.000

SU YILI (2006) YILLIK TOPLAM AKIM 18.86 MİLYON M3 0 MM. 0.0 LT/SN/Km2

15. Kizilirmak Havzasi

D15A224 CELEP D. ERSİL

YERİ : **KASTAMONU TAŞKÖPRÜ KARAYOLU ÜZERİNDEN ALATARLA'YA VARILDIKTAN SONRA BURADAN SAĞA DÖNÜLÜP 8 KM ILERIDE ERSIL KÖYÜNÜN MERKEZİNDEDİR.**
34°1'29" Doğu - 41°25'18" Kuzey

YAĞIŞ ALANI : **570,00 km2** **YAKLAŞIK KOT : 650 m**

GÖZLEM SÜRESİ : **10.12.1988 - 30.09.2006**

ORTALAMA AKIMLAR : **Gözlem süresinde 3.406 m3/sn. (12 Yıllık) 2006 Su yılında 2.324 m3/sn.**

ANLIK EN ÇOK VE EN AZ AKIMLAR:

2006 Su yılında anlık ençok akım	**:**	**14.2**	**m3/sn**	**25.03.2006**
2006 Su yılında anlık enaz akım	**:**	**0.220**	**m3/sn**	**20.08.2006**
Gözlem süresinde anlık ençok akım	**:**	**71.7**	**m3/sn**	**05.06.2000**
Gözlem süresinde anlık enaz akım	**:**	**0.046**	**m3/sn**	**19.10.2001**

100. Anahtar Eğrisi (Seviyeler cm olarak)

Seviye	Akım	Seviye	Akım	Seviye	Akım	Seviye	Akım
18	0.030	103	22.5	193	103.	332	347.
35	1.1	120	33.1	215	132.	371	442.
52	3.6	138	46.0	239	168.	414	561.
69	8.0	154	60.7	266	214.	463	712.
86	14.2	174	81.0	297	273.	517	906.

Akımlar 01 Ekim 2005 'den 30 Eylül 2006' a kadar m3/sn olarak

Gün	Ekim	Kasım	Aralık	Ocak	Şubat	Mart	Nisan	Mayıs	Haziran	Temmuz	Ağustos	Eylül
01	0.900	1.22	2.02	1.70	1.10	5.67	10.3	2.50	1.46	1.10	0.530	0.300
02	0.900	1.10	1.86	1.58	1.58	6.28	10.3	2.94	1.46	1.10	0.475	0.700
03	1.10	1.10	1.70	1.58	1.58	5.97	9.06	2.72	1.46	1.10	0.420	0.700
04	1.34	1.10	1.70	1.58	1.58	5.67	8.22	2.50	1.70	1.10	0.420	0.475
05	1.10	1.34	1.70	1.58	1.34	5.06	7.80	2.50	1.34	1.00	0.360	0.475
06	0.900	1.22	1.58	1.58	1.34	5.06	7.19	2.50	1.46	1.00	0.360	0.420
07	0.900	1.22	1.58	1.70	1.46	5.67	7.19	3.83	1.58	1.00	0.300	0.420
08	0.900	1.34	1.58	1.86	1.34	7.19	7.80	4.75	2.02	0.900	0.300	0.420
09	0.900	1.34	1.46	1.86	1.34	9.90	9.06	4.29	8.64	0.700	0.300	0.420
10	0.900	1.34	1.34	1.86	1.34	7.19	8.22	4.29	4.06	0.900	0.420	0.360
11	0.900	1.22	1.34	1.58	1.34	6.28	7.80	3.83	7.50	0.900	0.420	0.360
12	0.800	1.10	1.34	1.58	1.34	6.28	7.50	3.83	5.36	0.900	0.420	0.360
13	0.800	1.10	1.22	1.58	1.46	7.80	6.89	3.83	4.29	0.800	0.360	0.360
14	0.800	1.10	1.10	1.58	1.46	9.90	6.58	4.06	3.38	0.800	0.360	0.360
15	0.700	1.22	1.10	1.58	1.70	9.90	5.97	3.83	3.83	0.800	0.360	0.360
16	0.900	1.10	1.10	1.58	1.34	7.50	5.97	3.38	2.94	0.800	0.300	0.360
17	1.00	1.10	1.10	1.34	1.22	6.58	5.06	2.94	2.50	0.800	0.260	0.360
18	1.10	1.10	1.10	1.34	1.58	6.28	4.75	2.72	2.18	1.00	0.260	0.360
19	1.10	1.10	1.22	1.58	1.58	5.97	3.83	2.50	1.86	1.10	0.260	0.360
20	1.10	1.22	1.34	1.46	1.86	5.97	3.83	2.50	1.70	1.10	0.220	0.360
21	1.00	2.50	0.900	1.46	2.34	5.67	3.83	2.34	1.58	1.10	0.220	0.420
22	1.00	1.86	0.900	1.34	2.72	5.97	4.52	2.18	1.34	1.10	0.220	0.475
23	0.900	1.58	1.10	1.34	2.72	6.89	3.83	2.18	1.46	1.22	0.220	0.530
24	0.900	1.46	1.10	1.34	2.94	12.0	3.83	2.02	1.34	2.02	0.220	0.615
25	0.900	1.70	1.58	1.34	3.16	13.1	3.38	1.86	1.34	1.10	0.220	0.700
26	0.900	2.50	1.58	1.58	4.75	9.90	3.16	1.86	1.22	0.900	0.220	0.800
27	0.900	3.16	1.34	1.22	5.97	8.64	2.94	1.86	1.10	0.900	0.220	0.800
28	0.900	2.94	1.34	1.34	5.06	8.22	2.72	1.86	1.10	0.900	0.220	0.900
29	0.900	2.50	1.34	1.10	-----	7.80	2.50	1.70	1.10	0.900	0.260	0.800
30	1.00	2.34	1.46	1.10	-----	8.22	2.50	1.70	1.10	0.700	0.260	0.800
31	1.10	-----	1.46	1.10	-----	10.3	-----	1.46	-----	0.530	0.260	-----
Maks.	1.34	3.16	2.18	1.86	5.97	14.2	10.7	4.75	10.3	2.50	0.530	1.00
Min.	0.700	1.10	0.900	1.10	1.10	5.06	2.50	1.46	1.10	0.530	0.220	0.260
Ortalama	0.950	1.54	1.37	1.49	2.09	7.51	5.88	2.81	2.45	0.976	0.311	0.504
LT/SN/Km2	1.67	2.70	2.41	2.62	3.67	13.2	10.3	4.94	4.29	1.71	0.546	0.885
AKIM mm.	4.46	7.01	6.45	7.02	8.87	35.3	26.8	13.2	11.1	4.59	1.46	2.29
MİL. M3	2.54	3.99	3.68	4.00	5.06	20.1	15.3	7.54	6.34	2.62	0.833	1.31

SU YILI (2006) YILLIK TOPLAM AKIM 73.31 MİLYON M3 129 MM. 4.1 LT/SN/Km2

15. Kizilirmak Havzasi

D15A225 DADAY Ç. HASKÖY

YERİ : **KASTAMONU MERKEZ HASKÖY KÖYÜNDEDİR.**
33°50'32" Doğu - 41°27'11" Kuzey

YAĞIŞ ALANI : **1206,50 km2** **YAKLAŞIK KOT : 685 m**

GÖZLEM SÜRESİ : **10.06.1987 - 30.09.2006**

ORTALAMA AKIMLAR : **Gözlem süresinde 2.433 m3/sn. (12 Yıllık) 2006 Su yılında 1.499 m3/sn.**

ANLIK EN ÇOK VE EN AZ AKIMLAR:

2006 Su yılında anlık ençok akım	:	**10.2**	**m3/sn**	**27.02.2006**
2006 Su yılında anlık enaz akım	:	**0.087**	**m3/sn**	**16.08.2006**
Gözlem süresinde anlık ençok akım	:	**64.0**	**m3/sn**	**05.06.2000**
Gözlem süresinde anlık enaz akım	:	**0.000**	**m3/sn**	**01.10.1999**

Akımlar 01 Ekim 2005 'den 30 Eylül 2006' a kadar m3/sn olarak

Gün	Ekim	Kasım	Aralık	Ocak	Şubat	Mart	Nisan	Mayıs	Haziran	Temmuz	Ağustos	Eylül
01	1.25	0.953	1.12	1.04	1.25	7.49	2.85	1.88	0.870	0.248	0.175	0.175
02	1.25	0.953	1.12	1.12	1.12	8.99	2.85	1.88	0.870	0.248	0.175	0.703
03	1.25	0.953	1.12	1.12	1.12	8.20	2.69	1.88	0.786	0.248	0.175	0.703
04	1.12	1.04	1.04	1.25	1.25	8.20	2.69	1.88	0.786	0.248	0.175	0.619
05	1.04	1.25	1.12	1.12	1.12	7.73	2.69	1.88	0.619	0.248	0.139	0.452
06	0.953	0.953	1.12	1.25	1.12	6.28	2.69	1.88	0.536	0.369	0.175	0.369
07	0.870	0.953	1.12	1.25	1.25	6.54	2.69	2.00	0.285	0.369	0.175	0.452
08	0.786	0.953	1.12	1.12	1.25	6.78	2.69	2.00	0.786	0.285	0.248	0.452
09	0.786	0.953	1.12	1.12	1.25	7.49	2.69	1.88	2.00	0.212	0.369	0.369
10	0.870	0.953	1.12	1.25	1.25	5.76	2.69	1.88	1.50	0.212	0.285	0.369
11	0.870	0.953	1.12	1.12	1.37	4.99	2.54	1.88	1.50	0.212	0.285	0.369
12	1.12	0.953	1.25	1.25	1.50	4.73	2.38	1.88	1.62	0.212	0.285	0.369
13	0.953	0.953	1.25	1.12	1.37	6.02	2.25	2.13	1.62	0.212	0.285	0.369
14	1.04	0.953	1.25	1.04	1.25	7.02	2.13	2.38	1.62	0.175	0.285	0.369
15	1.04	1.25	1.25	1.25	1.25	6.28	2.00	1.88	1.62	0.175	0.285	0.369
16	1.04	1.12	1.12	1.25	1.25	5.25	2.00	1.88	1.62	0.175	0.212	0.369
17	1.04	1.04	1.12	1.12	1.25	4.99	2.00	1.75	1.37	0.175	0.175	0.369
18	0.953	0.953	1.04	1.12	1.25	4.99	2.00	1.75	1.12	0.175	0.175	0.369
19	0.953	0.953	1.50	1.12	1.37	4.99	2.00	1.62	1.12	0.139	0.102	0.369
20	1.12	1.25	1.37	1.12	1.75	4.73	2.00	1.37	0.953	0.139	0.102	0.369
21	0.953	1.37	1.12	1.12	2.13	4.73	2.00	1.37	0.786	0.139	0.102	0.369
22	0.953	1.12	1.04	1.25	2.69	4.47	2.00	1.37	0.786	0.175	0.248	0.369
23	0.953	1.12	1.12	1.25	3.48	4.47	2.13	1.12	0.786	0.212	0.452	0.369
24	0.870	1.12	1.25	1.25	4.99	4.21	2.13	1.04	0.536	0.285	0.452	0.452
25	0.786	1.12	1.12	1.25	7.25	3.79	2.13	0.953	0.285	0.369	0.452	0.703
26	0.786	1.12	1.12	1.25	7.49	3.64	2.13	1.04	0.285	0.285	0.452	0.452
27	0.870	1.25	1.25	1.25	9.62	3.32	2.00	1.04	0.248	0.285	0.452	0.452
28	0.870	1.25	1.12	1.12	7.97	3.17	1.88	0.953	0.248	0.248	0.452	0.452
29	0.870	1.12	1.04	1.04	-----	3.17	1.75	0.953	0.285	0.212	0.452	0.536
30	0.870	1.04	1.12	1.12	-----	3.01	2.00	0.870	0.285	0.175	0.248	0.536
31	0.870	-----	1.12	1.25	-----	2.85	-----	0.870	-----	0.175	0.139	-----
Maks.	1.37	1.50	2.00	1.37	10.2	9.62	2.85	2.54	4.21	0.369	0.452	0.786
Min.	0.786	0.870	1.04	0.953	1.04	2.85	1.75	0.870	0.248	0.102	0.087	0.102
Ortalama	0.966	1.06	1.16	1.17	2.54	5.43	2.29	1.59	0.924	0.227	0.264	0.435
LT/SN/Km2	0.801	0.882	0.957	0.971	2.11	4.50	1.90	1.31	0.766	0.188	0.219	0.360
AKIM mm.	2.15	2.29	2.56	2.60	5.10	12.1	4.92	3.52	1.99	0.504	0.586	0.934
MİL. M3	2.59	2.76	3.09	3.14	6.15	14.5	5.93	4.25	2.40	0.608	0.707	1.13

SU YILI (2006) YILLIK TOPLAM AKIM 47.26 MİLYON M3 39 MM. 1.2 LT/SN/Km2

15. Kizilirmak Havzasi

D15A226 DADAY Ç. GONCALAR

YERİ : **KASTAMONU-MERKEZ EYMÜR KÖYÜNDEDİR.**
33°35'48" Doğu - 41°28'40" Kuzey

YAĞIŞ ALANI : **462,50 km2** **YAKLAŞIK KOT : 805 m**

GÖZLEM SÜRESİ : **16.02.1987 - 30.09.2006**

ORTALAMA AKIMLAR : **Gözlem süresinde 1.458 m3/sn. (12 Yıllık) 2006 Su yılında 0.942 m3/sn.**

ANLIK EN ÇOK VE EN AZ AKIMLAR:

2006 Su yılında anlık ençok akım	:	**13.7**	**m3/sn**	**03.03.2006**
2006 Su yılında anlık enaz akım	:	**0.000**	**m3/sn**	**23.08.2006**
Gözlem süresinde anlık ençok akım	:	**64.0**	**m3/sn**	**17.04.2002**
Gözlem süresinde anlık enaz akım	:	**0.000**	**m3/sn**	**01.03.1999**

4. Anahtar Eğrisi (Seviyeler cm olarak)

Seviye	Akım	Seviye	Akım	Seviye	Akım	Seviye	Akım
1	0.007	25	1.0	110	16.5	200	49.0
4	0.045	40	2.5	140	25.0	210	54.0
7	0.115	60	5.3	170	36.0	220	59.0
10	0.203	75	8.1	180	40.0	230	64.0
16	0.474	90	11.0	190	44.0		

Akımlar 01 Ekim 2005 'den 30 Eylül 2006' a kadar m3/sn olarak

Gün	Ekim	Kasım	Aralık	Ocak	Şubat	Mart	Nisan	Mayıs	Haziran	Temmuz	Ağustos	Eylül
01	0.230	0.320	0.475	0.540	0.605	8.38	1.89	1.10	0.735	0.475	0.068	0.032
02	0.230	0.320	0.475	0.540	0.605	8.16	1.78	1.19	0.735	0.410	0.045	0.120
03	0.365	0.320	0.475	0.540	0.605	10.1	1.78	1.19	0.670	0.365	0.045	0.090
04	0.275	0.320	0.475	0.540	0.605	9.26	1.68	1.10	0.670	0.365	0.032	0.120
05	0.275	0.320	0.475	0.540	0.540	5.94	1.57	1.03	0.605	0.365	0.019	0.120
06	0.275	0.320	0.475	0.605	0.540	5.05	1.57	1.03	0.605	0.365	0.013	0.120
07	0.275	0.320	0.475	0.605	0.605	5.40	1.48	1.10	0.605	0.365	0.013	0.120
08	0.275	0.320	0.475	0.540	0.605	6.13	1.48	1.19	0.605	0.365	0.013	0.090
09	0.230	0.320	0.475	0.540	0.605	6.13	1.38	1.10	0.670	0.320	0.045	0.090
10	0.230	0.320	0.475	0.540	0.605	4.36	1.38	1.10	0.808	0.320	0.032	0.032
11	0.230	0.320	0.475	0.540	0.605	3.85	1.38	1.10	0.808	0.320	0.019	0.068
12	0.230	0.320	0.410	0.605	0.670	3.85	1.38	1.10	0.808	0.275	0.045	0.068
13	0.230	0.320	0.410	0.605	0.670	5.22	1.29	1.29	0.735	0.230	0.032	0.068
14	0.230	0.320	0.410	0.605	0.670	5.76	1.29	1.38	0.808	0.230	0.001	0.068
15	0.230	0.410	0.410	0.605	0.670	4.87	1.29	1.29	0.808	0.275	0.006	0.068
16	0.275	0.365	0.475	0.605	0.881	3.85	1.29	1.19	0.808	0.275	0.013	0.068
17	0.275	0.365	0.475	0.605	1.10	3.46	1.29	1.19	0.735	0.275	0.013	0.068
18	0.275	0.365	0.475	0.605	0.670	3.33	1.29	1.19	0.670	0.230	0.013	0.068
19	0.275	0.365	0.540	0.605	0.670	3.20	1.29	1.10	0.670	0.230	0.004	0.068
20	0.475	0.410	0.540	0.670	1.03	2.87	1.29	1.03	0.670	0.190	0.013	0.068
21	0.365	0.475	0.475	0.670	1.48	2.76	1.29	1.03	0.670	0.190	0.001	0.068
22	0.320	0.410	0.475	0.670	2.21	2.65	1.19	0.954	0.670	0.190	KURU	0.090
23	0.320	0.410	0.475	0.605	2.87	2.76	1.19	0.954	0.670	0.190	KURU	0.090
24	0.320	0.410	0.475	0.605	3.20	3.20	1.19	0.881	0.540	0.150	0.006	0.150
25	0.275	0.410	0.475	0.670	3.33	2.98	1.10	0.881	0.475	0.120	0.013	0.150
26	0.320	0.410	0.475	0.670	6.70	2.65	1.10	0.881	0.475	0.120	0.019	0.150
27	0.320	0.410	0.475	0.605	8.38	2.43	1.10	0.881	0.540	0.090	0.004	0.120
28	0.320	0.410	0.475	0.605	7.50	2.21	1.10	0.881	0.540	0.068	0.013	0.120
29	0.320	0.475	0.475	0.670	-----	2.10	1.10	0.808	0.540	0.068	0.019	0.120
30	0.320	0.475	0.475	0.954	-----	1.99	1.10	0.808	0.475	0.090	0.019	0.120
31	0.320	-----	0.540	0.808	-----	1.99	-----	0.735	-----	0.090	0.013	-----
Maks.	0.475	0.475	0.540	1.48	9.26	13.7	1.89	1.38	0.808	0.475	0.090	0.150
Min.	0.230	0.320	0.410	0.540	0.540	1.89	1.10	0.735	0.475	0.045	KURU	0.004
Ortalama	0.287	0.369	0.473	0.617	1.76	4.42	1.35	1.05	0.661	0.246	0.019	0.093
LT/SN/Km2	0.621	0.797	1.02	1.33	3.80	9.55	2.92	2.28	1.43	0.531	0.041	0.201
AKIM mm.	1.66	2.07	2.74	3.57	9.20	25.6	7.57	6.11	3.70	1.42	0.110	0.522
MİL. M3	0.769	0.955	1.27	1.65	4.25	11.8	3.50	2.82	1.71	0.658	0.051	0.241

SU YILI (2006) YILLIK TOPLAM AKIM 29.67 MİLYON M3 64 MM. 2.0 LT/SN/Km2

15. Kizilirmak Havzasi

D15A227 KARA D. DELİLER

YERİ : KASTAMONU- MERKEZ DELİLER KÖYÜNDEDIR.
33°57'12" Doğu - 41°23'32" Kuzey

YAĞIŞ ALANI : 280,00 km2 **YAKLAŞIK KOT :** 710 m

GÖZLEM SÜRESİ : 11.06.1987 - 30.09.2006

ORTALAMA AKIMLAR : Gözlem süresinde 1.885 m3/sn. (13 Yıllık) 2006 Su yılında 1.064 m3/sn.

ANLIK EN ÇOK VE EN AZ AKIMLAR:

2006 Su yılında anlık ençok akım	:	7.50	m3/sn	11.06.2006
2006 Su yılında anlık enaz akım	:	0.050	m3/sn	18.08.2006
Gözlem süresinde anlık ençok akım	:	38.8	m3/sn	23.04.2004
Gözlem süresinde anlık enaz akım	:	0.000	m3/sn	01.10.1990

2. Anahtar Eğrisi (Seviyeler cm olarak)

Seviye	Akım	Seviye	Akım	Seviye	Akım	Seviye	Akım
33	0.004	60	3.2	110	16.5	160	31.0
36	0.027	70	5.8	120	19.5	170	34.0
38	0.110	80	8.8	130	23.0	180	37.0
40	0.220	90	11.5	140	25.0	190	40.0
50	1.3	100	14.0	150	28.0	200	43.0

Akımlar 01 Ekim 2005 'den 30 Eylül 2006' a kadar m3/sn olarak

Gün	Ekim	Kasım	Aralık	Ocak	Şubat	Mart	Nisan	Mayıs	Haziran	Temmuz	Ağustos	Eylül
01	0.280	0.440	0.953	0.720	0.580	3.02	3.50	1.73	0.795	0.580	0.280	0.095
02	0.245	0.510	0.870	0.795	0.440	3.02	3.50	2.00	0.720	0.580	0.245	0.370
03	0.280	0.440	0.870	0.720	0.440	3.18	3.18	2.00	0.650	0.510	0.245	0.405
04	0.310	0.440	0.795	0.720	0.510	3.02	3.02	1.73	0.650	0.440	0.220	0.370
05	0.310	0.510	0.795	0.720	0.440	2.56	2.86	1.73	0.580	0.405	0.180	0.310
06	0.280	0.510	0.720	0.720	0.440	2.56	2.70	1.60	0.510	0.405	0.180	0.310
07	0.280	0.510	0.720	0.795	0.440	3.02	2.86	1.73	0.510	0.440	0.150	0.280
08	0.280	0.510	0.720	0.870	0.440	3.80	3.18	2.86	0.440	0.580	0.130	0.280
09	0.245	0.510	0.650	0.720	0.440	4.40	3.34	2.56	1.20	0.580	0.130	0.280
10	0.245	0.440	0.650	0.720	0.440	3.02	3.34	2.56	2.14	0.580	0.130	0.245
11	0.245	0.440	0.650	0.720	0.440	2.70	3.18	2.42	2.42	0.510	0.110	0.245
12	0.245	0.440	0.580	0.720	0.510	2.86	3.18	2.28	2.28	0.440	0.095	0.280
13	0.245	0.405	0.580	0.720	0.510	4.10	3.18	2.28	1.60	0.440	0.095	0.245
14	0.245	0.405	0.510	0.650	0.440	5.20	3.02	2.42	1.60	0.405	0.095	0.220
15	0.245	0.440	0.510	0.650	0.510	4.40	3.34	2.14	1.60	0.405	0.095	0.220
16	0.245	0.440	0.510	0.580	0.510	3.34	2.86	1.87	1.73	0.370	0.075	0.220
17	0.310	0.440	0.440	0.510	0.650	2.86	2.56	1.87	1.60	0.370	0.060	0.180
18	0.310	0.440	0.510	0.510	0.580	2.70	2.42	1.73	1.33	0.580	0.060	0.180
19	0.310	0.440	0.510	0.510	0.580	2.70	2.42	1.60	1.12	0.510	0.060	0.150
20	0.310	0.440	0.580	0.580	0.580	2.56	2.42	1.73	1.04	0.440	0.075	0.180
21	0.310	1.20	0.510	0.510	0.720	2.56	2.56	1.60	0.953	0.405	0.075	0.180
22	0.310	0.953	0.510	0.580	0.953	2.56	2.56	1.47	0.870	0.405	0.075	0.280
23	0.310	0.720	0.510	0.580	1.04	2.86	2.42	1.33	0.795	0.405	0.075	0.245
24	0.310	0.720	0.510	0.580	1.12	5.00	2.42	1.33	0.795	0.510	0.075	0.280
25	0.310	0.720	0.510	0.580	1.33	5.20	2.28	1.20	0.795	0.580	0.095	0.510
26	0.280	1.47	0.510	0.580	2.42	3.50	2.14	1.12	0.720	0.510	0.110	0.580
27	0.280	1.47	0.510	0.580	2.86	3.18	2.00	1.12	0.650	0.440	0.110	0.440
28	0.280	1.33	0.580	0.510	2.56	3.02	1.87	1.12	0.580	0.405	0.110	0.405
29	0.280	1.12	0.650	0.580	-----	3.02	1.73	1.04	0.580	0.370	0.110	0.370
30	0.280	1.12	0.650	0.580	-----	3.18	1.73	1.04	0.580	0.310	0.110	0.370
31	0.370	-----	0.650	0.650	-----	4.10	-----	0.953	-----	0.280	0.095	-----
Maks.	0.440	1.60	1.12	0.870	3.18	6.30	4.10	3.34	7.50	1.20	0.280	1.04
Min.	0.245	0.370	0.370	0.245	0.280	2.42	1.73	0.870	0.440	0.150	0.050	0.095
Ortalama	0.283	0.666	0.620	0.644	0.819	3.33	2.73	1.75	1.06	0.458	0.121	0.291
LT/SN/Km2	1.01	2.38	2.21	2.30	2.92	11.9	9.73	6.24	3.79	1.63	0.432	1.04
AKIM mm.	2.71	6.16	5.93	6.16	7.07	31.8	25.2	16.7	9.82	4.38	1.16	2.69
MİL. M3	0.759	1.73	1.66	1.72	1.98	8.92	7.06	4.68	2.75	1.23	0.324	0.754

SU YILI (2006) YILLIK TOPLAM AKIM 33.57 MİLYON M3 120 MM. 3.8 LT/SN/Km2

15. Kizilirmak Havzasi

D15A233 YAHYALI SUYU YAHYALI

YERİ : **KAYSERİ İLİ YAHYALI İLÇESİ HÜKÜMET MEYDANI ATATÜRK HEYKELİNE 100 M MESAFEDE MEMBAA İSTİKAMETİNDEDİR.**
35°21'39" Doğu - 38°5'54" Kuzey

YAĞIŞ ALANI : **145,20 km2** **YAKLAŞIK KOT : 1128 m**

GÖZLEM SÜRESİ : **01.10.1988 - 30.09.2006**

ORTALAMA AKIMLAR : **Gözlem süresinde 1.478 m3/sn. (12 Yıllık) 2006 Su yılında 0.885 m3/sn.**

ANLIK EN ÇOK VE EN AZ AKIMLAR:

2006 Su yılında anlık ençok akım	:	**6.56**	**m3/sn**	**15.06.2006**
2006 Su yılında anlık enaz akım	:	**0.003**	**m3/sn**	**15.11.2005**
Gözlem süresinde anlık ençok akım	:	**25.2**	**m3/sn**	**13.04.1992**
Gözlem süresinde anlık enaz akım	:	**0.000**	**m3/sn**	**23.09.1992**

İstasyon için kullanılmış anahtar bulunamadı.

Akımlar 01 Ekim 2005 'den 30 Eylül 2006' a kadar m3/sn olarak

Gün	Ekim	Kasım	Aralık	Ocak	Şubat	Mart	Nisan	Mayıs	Haziran	Temmuz	Ağustos	Eylül
01	0.179	0.179	0.379	0.146	0.102	0.285	2.02	3.80	1.93	0.721	0.379	0.639
02	0.179	0.179	0.379	0.146	0.102	0.379	2.20	3.95	1.93	0.639	0.379	0.639
03	0.179	0.179	0.379	0.146	0.102	0.474	2.59	3.95	1.93	0.639	0.379	0.639
04	0.179	0.179	0.285	0.146	0.102	0.721	2.98	3.95	1.93	0.474	0.379	0.721
05	0.179	0.179	0.285	0.146	0.102	0.556	2.78	3.95	1.93	0.379	0.379	0.639
06	0.179	0.179	0.285	0.146	0.102	0.556	2.39	3.64	1.93	0.379	0.379	0.721
07	0.179	0.179	0.285	0.146	0.102	0.721	2.39	3.48	1.93	0.379	0.285	0.639
08	0.179	0.179	0.379	0.146	0.102	0.804	2.78	3.33	1.93	0.379	0.190	0.639
09	0.179	0.179	0.379	0.146	0.102	0.721	2.98	2.98	1.93	0.379	0.190	0.639
10	0.179	0.179	0.379	0.146	0.102	0.804	3.80	2.78	1.84	0.379	0.190	0.639
11	0.179	0.179	0.379	0.146	0.102	0.639	4.11	2.59	1.84	0.379	0.190	0.639
12	0.179	0.179	0.379	0.146	0.102	0.556	3.80	2.59	1.84	0.379	0.190	0.556
13	0.179	0.179	0.379	0.146	0.102	0.639	3.95	2.59	1.84	0.379	0.190	0.556
14	0.179	0.179	0.379	0.146	0.102	0.721	3.95	2.59	1.84	0.379	0.379	0.556
15	0.179	0.179	0.379	0.146	0.102	0.804	3.95	2.39	0.556	0.379	0.379	0.556
16	0.179	0.179	0.556	0.146	0.102	0.804	3.80	2.20	0.556	0.379	0.379	0.556
17	0.179	0.124	0.556	0.146	0.102	0.886	3.64	2.39	0.556	0.379	0.379	0.556
18	0.179	0.474	0.474	0.146	0.102	0.886	3.64	2.20	0.556	0.379	0.379	0.556
19	0.179	0.190	0.474	0.190	0.102	1.01	3.33	2.11	0.556	0.379	0.146	0.556
20	0.179	0.190	0.474	0.190	0.102	1.01	2.98	2.11	0.556	0.379	0.190	0.639
21	0.179	0.190	0.474	0.190	0.102	0.886	3.17	2.02	0.556	0.379	0.379	0.639
22	0.179	0.285	0.474	0.190	0.102	1.13	2.98	2.02	0.556	0.379	0.379	0.639
23	0.179	0.285	0.474	0.190	0.102	1.84	2.78	2.02	0.474	0.379	0.379	0.639
24	0.179	0.285	0.474	0.190	0.285	2.20	2.78	2.02	0.474	0.379	0.379	0.721
25	0.179	0.285	0.474	0.190	0.285	2.39	2.78	2.02	0.474	0.379	0.474	0.639
26	0.179	0.285	0.474	0.190	0.379	2.39	2.78	2.02	0.474	0.379	0.639	0.639
27	0.179	0.285	0.474	0.190	0.474	2.02	2.98	2.02	0.474	0.379	0.639	0.639
28	0.179	0.285	0.474	0.190	0.379	1.93	3.17	2.02	0.474	0.379	0.639	0.639
29	0.179	0.379	0.474	0.190	-----	1.84	3.17	2.02	0.556	0.379	0.639	0.639
30	0.179	0.379	0.474	0.190	-----	1.75	3.48	2.02	0.721	0.379	0.639	0.556
31	0.179	-----	0.474	0.190	-----	2.02	-----	1.93	-----	0.379	0.639	-----
Maks.	0.179	4.11	0.886	0.190	0.474	2.59	4.57	4.80	6.56	1.63	1.75	1.13
Min.	0.179	0.003	0.190	0.146	0.102	0.285	1.93	1.93	0.474	0.379	0.146	0.474
Ortalama	0.179	0.226	0.421	0.164	0.148	1.11	3.14	2.64	1.17	0.410	0.379	0.622
LT/SN/Km2	1.23	1.56	2.90	1.13	1.02	7.64	21.6	18.2	8.07	2.82	2.61	4.29
AKIM mm.	3.30	4.04	7.77	3.03	2.47	20.5	56.0	48.6	20.9	7.56	6.99	11.1
MİL. M3	0.479	0.586	1.13	0.440	0.358	2.97	8.13	7.06	3.04	1.10	1.02	1.61

SU YILI (2006) YILLIK TOPLAM AKIM 27.92 MİLYON M3 192 MM. 6.1 LT/SN/Km2

15. Kizilirmak Havzasi

D15A236 AKCAKIŞLA DERESİ BOZKURT

YERİ : **SİVAS ŞARKIŞLA İLÇESİ BOZKURT KÖYÜ ÇIKIŞINDADIR**
36°22'23" Doğu - 39°30'34" Kuzey

YAĞIŞ ALANI : **414,20 km2** **YAKLAŞIK KOT : 1210 m**

GÖZLEM SÜRESİ : **08.09.1987 - 30.09.2006**

ORTALAMA AKIMLAR : **Gözlem süresinde 1.094 m3/sn. (18 Yıllık) 2006 Su yılında 0.589 m3/sn.**

ANLIK EN ÇOK VE EN AZ AKIMLAR:

2006 Su yılında anlık ençok akım	:	**2.70**	**m3/sn**	**25.03.2006**
2006 Su yılında anlık enaz akım	:	**0.002**	**m3/sn**	**12.08.2006**
Gözlem süresinde anlık ençok akım	:	**30.5**	**m3/sn**	**16.05.1991**
Gözlem süresinde anlık enaz akım	:	**0.000**	**m3/sn**	**29.08.1994**

Akımlar 01 Ekim 2005 'den 30 Eylül 2006' a kadar m3/sn olarak

Gün	Ekim	Kasım	Aralık	Ocak	Şubat	Mart	Nisan	Mayıs	Haziran	Temmuz	Ağustos	Eylül
01	0.003	0.424	0.478	0.478	0.478	0.844	1.55	1.80	0.980	0.127	0.005	0.002
02	0.003	0.424	0.478	0.478	0.478	0.912	2.10	2.00	0.912	0.127	0.004	0.002
03	0.004	0.424	0.478	0.478	0.532	0.912	2.20	2.20	0.844	0.127	0.005	0.003
04	0.005	0.424	0.478	0.478	0.532	1.06	2.00	2.10	0.586	0.101	0.005	0.003
05	0.008	0.424	0.478	0.478	0.532	0.912	1.90	2.00	0.532	0.048	0.005	0.003
06	0.008	0.424	0.478	0.478	0.532	0.912	1.72	1.90	0.478	0.074	0.004	0.003
07	0.008	0.424	0.478	0.532	0.532	0.980	1.64	1.80	0.424	0.101	0.004	0.002
08	0.008	0.424	0.478	0.532	0.532	1.14	1.64	2.20	0.370	0.127	0.004	0.002
09	0.008	0.424	0.478	0.532	0.586	1.23	1.64	2.00	0.370	0.101	0.004	0.002
10	0.011	0.424	0.478	0.478	0.532	1.06	1.64	2.00	0.332	0.074	0.004	0.002
11	0.016	0.478	0.478	0.532	0.640	0.980	1.72	1.90	0.154	0.020	0.004	0.002
12	0.016	0.532	0.478	0.478	0.844	0.980	1.64	1.72	0.074	0.011	0.003	0.002
13	0.016	0.532	0.478	0.478	0.844	0.980	1.64	1.80	0.034	0.020	0.003	0.003
14	0.016	0.532	0.424	0.478	0.776	0.980	1.55	1.80	0.020	0.016	0.003	0.003
15	0.020	0.478	0.478	0.478	0.776	1.06	1.55	1.64	0.020	0.011	0.003	0.003
16	0.034	0.478	0.586	0.478	0.708	0.980	1.72	1.72	0.034	0.016	0.003	0.002
17	0.034	0.478	0.640	0.478	0.708	1.06	1.55	2.10	0.048	0.034	0.003	0.002
18	0.034	0.478	0.586	0.478	0.708	0.980	1.55	1.80	0.048	0.034	0.003	0.004
19	0.048	0.478	0.586	0.478	0.640	0.980	1.47	1.80	0.034	0.020	0.003	0.005
20	0.074	0.478	0.586	0.478	0.640	0.980	1.39	1.64	0.020	0.016	0.003	0.003
21	0.074	0.532	0.586	0.424	0.640	0.980	1.47	1.55	0.020	0.011	0.003	0.005
22	0.101	0.532	0.532	0.424	0.640	1.23	1.47	1.47	0.034	0.034	0.003	0.020
23	0.127	0.478	0.532	0.424	0.640	1.23	1.55	1.47	0.034	0.016	0.002	0.101
24	0.127	0.478	0.532	0.370	0.640	1.14	1.90	1.47	0.016	0.016	0.002	0.127
25	0.127	0.478	0.532	0.370	0.708	1.90	2.00	1.39	0.016	0.016	0.002	0.127
26	0.154	0.478	0.478	0.478	0.776	2.10	1.80	1.31	0.020	0.008	0.002	0.127
27	0.154	0.532	0.478	0.478	0.776	1.90	1.72	1.55	0.016	0.008	0.002	0.127
28	0.180	0.532	0.478	0.478	0.844	1.72	1.64	1.47	0.016	0.008	0.002	0.101
29	0.180	0.478	0.478	0.478	-----	1.64	1.55	1.31	0.074	0.008	0.002	0.074
30	0.256	0.478	0.424	0.478	-----	1.55	2.00	1.23	0.154	0.008	0.002	0.101
31	0.370	-----	0.424	0.478	-----	1.55	-----	1.14	-----	0.005	0.002	-----
Maks.	0.370	0.776	0.640	0.640	0.980	2.70	2.40	2.50	1.14	0.180	0.005	1.47
Min.	0.003	0.332	0.424	0.370	0.424	0.776	1.31	0.980	0.011	0.005	0.002	0.002
Ortalama	0.072	0.473	0.502	0.473	0.651	1.19	1.70	1.72	0.224	0.043	0.003	0.032
LT/SN/Km2	0.173	1.14	1.21	1.14	1.57	2.87	4.10	4.15	0.540	0.105	0.008	0.077
AKIM mm.	0.464	2.96	3.25	3.06	3.80	7.69	10.6	11.1	1.40	0.280	0.021	0.201
MİL. M3	0.192	1.22	1.35	1.27	1.57	3.18	4.40	4.60	0.580	0.116	0.009	0.083

SU YILI (2006) YILLIK TOPLAM AKIM 18.57 MİLYON M3 45 MM. 1.4 LT/SN/Km2

15. Kizilirmak Havzasi

D15A243 KOLAZ Ç. KALEBAĞI

YERİ : **BOYABAT İLÇE MERKEZİNİN KALEBAĞI MEVKİ, BELEDİYENİN MESİRE ALANININ HEMEN YANINDADIR**
25 LİK PAFTADAKİ YERİ: F33-B1
34°45'12" Doğu - 41°27'54" Kuzey

YAĞIŞ ALANI : **659,00 km2** **YAKLAŞIK KOT : 316 m**

GÖZLEM SÜRESİ : **11.10.1989 - 30.09.2006**

ORTALAMA AKIMLAR : **Gözlem süresinde 1.586 m3/sn. (15 Yıllık) 2006 Su yılında 0.956 m3/sn.**

ANLIK EN ÇOK VE EN AZ AKIMLAR:

2006 Su yılında anlık ençok akım	**:**	**9.25**	**m3/sn**	**03.03.2006**
2006 Su yılında anlık enaz akım	**:**	**0.000**	**m3/sn**	**08.06.2006**
Gözlem süresinde anlık ençok akım	**:**	**118.**	**m3/sn**	**23.04.2004**
Gözlem süresinde anlık enaz akım	**:**	**0.000**	**m3/sn**	**01.10.1989**

10. Anahtar Eğrisi (Seviyeler cm olarak)

Akımlar 01 Ekim 2005 'den 30 Eylül 2006' a kadar m3/sn olarak

Gün	Ekim	Kasım	Aralık	Ocak	Şubat	Mart	Nisan	Mayıs	Haziran	Temmuz	Ağustos	Eylül
01	0.040	0.090	0.560	0.220	0.335	5.40	4.20	0.803	0.803	0.001	KURU	KURU
02	0.015	0.090	0.560	0.335	0.335	5.16	4.20	0.935	0.803	KURU	KURU	KURU
03	0.015	0.090	0.560	0.335	0.220	5.66	4.20	0.803	0.803	KURU	KURU	KURU
04	0.020	0.090	0.560	0.335	0.335	7.48	3.72	0.803	0.803	KURU	KURU	KURU
05	0.020	0.335	0.450	0.335	0.335	7.74	3.24	0.803	1.38	KURU	KURU	KURU
06	0.015	0.450	0.450	0.335	0.335	7.48	3.24	0.803	1.74	KURU	KURU	KURU
07	0.015	0.450	0.450	0.335	0.450	7.48	3.24	0.935	0.065	KURU	KURU	KURU
08	0.030	0.335	0.450	0.450	0.450	7.48	3.00	2.82	KURU	KURU	KURU	KURU
09	0.030	0.335	0.335	0.450	0.450	8.00	3.00	2.82	0.003	KURU	KURU	KURU
10	0.030	0.335	0.335	0.450	0.450	7.48	3.00	2.28	0.020	KURU	KURU	KURU
11	0.020	0.335	0.335	0.450	0.450	7.48	2.82	2.10	0.030	KURU	KURU	KURU
12	0.040	0.335	0.335	0.450	0.560	6.70	2.64	2.10	0.065	KURU	KURU	KURU
13	0.065	0.335	0.335	0.450	0.560	6.18	2.46	2.10	0.040	KURU	KURU	KURU
14	0.065	0.220	0.335	0.450	0.450	5.40	2.28	2.64	0.065	KURU	KURU	0.155
15	0.065	0.335	0.335	0.450	0.560	4.44	2.28	2.28	0.065	KURU	KURU	1.74
16	0.065	0.335	0.335	0.335	0.335	3.96	2.28	1.92	0.065	KURU	KURU	1.56
17	0.065	0.335	0.335	0.155	0.335	3.96	2.28	1.92	0.040	KURU	KURU	1.38
18	0.065	0.335	0.335	0.335	0.560	3.48	2.28	1.92	0.030	KURU	KURU	0.935
19	0.090	0.335	0.335	0.335	0.560	3.48	2.28	1.92	0.020	KURU	KURU	0.006
20	0.090	0.335	0.450	0.335	0.670	3.48	1.92	1.92	0.008	KURU	KURU	0.001
21	0.090	0.450	0.220	0.220	0.803	3.48	1.74	1.38	0.008	KURU	KURU	0.015
22	0.090	0.560	0.220	0.335	1.07	3.00	1.74	0.935	0.008	KURU	KURU	0.006
23	0.090	0.560	0.220	0.335	1.74	2.82	1.38	0.935	0.008	KURU	KURU	0.008
24	0.090	0.560	0.220	0.335	1.74	3.48	1.07	0.803	0.008	KURU	KURU	0.008
25	0.090	0.560	0.220	0.220	2.10	4.20	0.935	0.803	0.008	KURU	KURU	0.020
26	0.065	0.560	0.220	0.220	3.96	3.96	0.935	0.803	0.008	KURU	KURU	0.020
27	0.065	0.560	0.220	0.220	5.16	3.96	0.935	0.803	0.006	KURU	KURU	0.030
28	0.065	0.560	0.220	0.335	4.92	3.72	0.935	0.803	0.001	KURU	KURU	0.030
29	0.065	0.560	0.220	0.155	-----	3.72	0.803	0.803	0.001	KURU	KURU	0.030
30	0.065	0.560	0.220	0.090	-----	3.72	0.803	0.803	0.001	KURU	KURU	0.030
31	0.090	-----	0.220	0.155	-----	4.20	-----	0.803	-----	KURU	KURU	-----
Maks.	0.090	0.560	0.560	0.450	5.66	9.25	4.20	3.48	2.46	0.008	KURU	2.10
Min.	0.010	0.090	0.155	0.065	0.155	2.82	0.803	0.803	KURU	KURU	KURU	KURU
Ortalama	0.056	0.378	0.342	0.321	1.08	5.10	2.33	1.43	0.230	0.000	KURU	0.199
LT/SN/Km2	0.084	0.573	0.519	0.487	1.64	7.74	3.53	2.17	0.349	0.000	0.000	0.302
AKIM mm.	0.226	1.48	1.39	1.30	3.96	20.7	9.16	5.81	0.905	0.000	0.000	0.783
MİL. M3	0.149	0.978	0.915	0.859	2.61	13.7	6.03	3.83	0.597	0.000	0.000	0.516

SU YILI (2006) YILLIK TOPLAM AKIM 30.18 MİLYON M3 46 MM. 1.5 LT/SN/Km2

15. Kizilirmak Havzasi

D15A249 YAHYASARAY BARAJ GİRİŞİ KANAK ÇAYI

YERİ : YOZGAT İLİ SARIKAYA İLÇESİ YUKARI YAHYASARAY KÖYÜNDEDİR.
35°46'32" Doğu - 39°30'30" Kuzey

YAĞIŞ ALANI : 131,08 km2 **YAKLAŞIK KOT :** 1387 m

GÖZLEM SÜRESİ : 01.10.1990 - 30.09.2006

ORTALAMA AKIMLAR : Gözlem süresinde 0.508 m3/sn. (16 Yıllık) 2006 Su yılında 0.244 m3/sn.

ANLIK EN ÇOK VE EN AZ AKIMLAR:

2006 Su yılında anlık ençok akım	:	0.860 m3/sn	23.04.2006
2006 Su yılında anlık enaz akım	:	0.012 m3/sn	08.08.2006
Gözlem süresinde anlık ençok akım	:	10.2 m3/sn	05.03.2004
Gözlem süresinde anlık enaz akım	:	0.000 m3/sn	25.07.2001

1. Anahtar Eğrisi (Seviyeler cm olarak)

Seviye	Akım	Seviye	Akım	Seviye	Akım	Seviye	Akım
1	0.000	11	0.110	21	0.550	71	6.0
3	0.000	13	0.180	31	1.2	81	7.4
5	0.000	15	0.250	41	2.2	91	9.0
7	0.023	17	0.360	51	3.3	97	10.2
9	0.058	19	0.450	61	4.6	101	11.9

Akımlar 01 Ekim 2005 'den 30 Eylül 2006' a kadar m3/sn olarak

Gün	Ekim	Kasım	Aralık	Ocak	Şubat	Mart	Nisan	Mayıs	Haziran	Temmuz	Ağustos	Eylül
01	0.250	0.220	0.250	0.305	0.305	0.305	0.450	0.410	0.250	0.110	0.038	0.023
02	0.250	0.220	0.250	0.305	0.305	0.305	0.550	0.450	0.250	0.110	0.038	0.023
03	0.250	0.250	0.250	0.305	0.305	0.305	0.550	0.450	0.250	0.084	0.023	0.038
04	0.250	0.250	0.250	0.305	0.360	0.360	0.500	0.410	0.220	0.084	0.023	0.038
05	0.305	0.250	0.250	0.305	0.360	0.360	0.450	0.410	0.220	0.084	0.023	0.023
06	0.250	0.250	0.250	0.305	0.360	0.360	0.450	0.410	0.220	0.084	0.023	0.023
07	0.250	0.250	0.305	0.305	0.450	0.360	0.450	0.410	0.180	0.084	0.023	0.038
08	0.220	0.220	0.305	0.305	0.410	0.360	0.410	0.450	0.180	0.084	0.023	0.023
09	0.220	0.220	0.305	0.305	0.410	0.360	0.410	0.410	0.180	0.084	0.012	0.023
10	0.220	0.220	0.305	0.305	0.410	0.450	0.410	0.410	0.180	0.084	0.012	0.023
11	0.220	0.220	0.360	0.305	0.360	0.450	0.410	0.410	0.220	0.058	0.012	0.038
12	0.220	0.220	0.360	0.305	0.360	0.410	0.410	0.410	0.250	0.038	0.012	0.038
13	0.220	0.220	0.360	0.305	0.360	0.410	0.410	0.410	0.220	0.058	0.023	0.038
14	0.220	0.220	0.360	0.305	0.360	0.410	0.410	0.410	0.220	0.058	0.023	0.038
15	0.220	0.220	0.305	0.305	0.305	0.450	0.450	0.410	0.180	0.058	0.023	0.038
16	0.220	0.220	0.305	0.305	0.305	0.450	0.450	0.410	0.180	0.058	0.023	0.038
17	0.220	0.220	0.305	0.305	0.305	0.450	0.450	0.450	0.140	0.058	0.023	0.038
18	0.220	0.220	0.305	0.305	0.305	0.450	0.410	0.450	0.140	0.038	0.023	0.038
19	0.220	0.220	0.305	0.305	0.305	0.450	0.410	0.410	0.110	0.038	0.023	0.038
20	0.220	0.250	0.250	0.305	0.305	0.450	0.410	0.410	0.110	0.038	0.023	0.058
21	0.220	0.250	0.250	0.305	0.305	0.450	0.410	0.410	0.110	0.038	0.023	0.058
22	0.220	0.250	0.305	0.305	0.305	0.450	0.360	0.410	0.110	0.038	0.023	0.038
23	0.220	0.250	0.305	0.305	0.305	0.450	0.410	0.360	0.110	0.058	0.023	0.058
24	0.220	0.250	0.305	0.305	0.305	0.450	0.450	0.305	0.110	0.038	0.023	0.058
25	0.220	0.250	0.305	0.305	0.305	0.450	0.450	0.305	0.110	0.038	0.023	0.058
26	0.220	0.250	0.305	0.305	0.305	0.450	0.410	0.305	0.084	0.038	0.023	0.084
27	0.220	0.250	0.305	0.305	0.305	0.450	0.410	0.410	0.084	0.038	0.023	0.084
28	0.220	0.250	0.305	0.305	0.305	0.500	0.410	0.360	0.110	0.038	0.023	0.058
29	0.220	0.250	0.305	0.305	-----	0.450	0.410	0.305	0.110	0.058	0.023	0.038
30	0.220	0.250	0.305	0.305	-----	0.450	0.450	0.305	0.140	0.058	0.023	0.038
31	0.220	-----	0.305	0.305	-----	0.450	-----	0.305	-----	0.038	0.023	-----
Maks.	0.305	0.305	0.410	0.305	0.500	0.550	0.860	0.550	0.305	0.140	0.038	0.084
Min.	0.220	0.220	0.220	0.305	0.250	0.305	0.360	0.250	0.084	0.023	0.012	0.023
Ortalama	0.229	0.236	0.298	0.305	0.335	0.416	0.434	0.393	0.166	0.060	0.023	0.042
LT/SN/Km2	1.74	1.80	2.27	2.33	2.56	3.18	3.31	3.00	1.27	0.460	0.172	0.317
AKIM mm.	4.67	4.67	6.09	6.23	6.19	8.51	8.58	8.03	3.28	1.23	0.461	0.822
MİL. M3	0.612	0.612	0.798	0.817	0.811	1.11	1.12	1.05	0.430	0.162	0.060	0.108

SU YILI (2006) YILLIK TOPLAM AKIM 7.69 MİLYON M3 59 MM. 1.9 LT/SN/Km2

15. Kizilirmak Havzasi

D15A254 KAYMAL D. KURUSARAY

YERİ : **SİNOP-BOYABAT - KURUSARAY KÖYÜNÜN 1.5 KM BATISINDA KAYMAL DERESİ ÜZERİNDEKİ KÖPRÜNÜN MEMBAINDADIR. 25 LİK PAFTADAKİ YERİ: F33-A2**
34°38'29" Doğu - 41°28'32" Kuzey

YAĞIŞ ALANI : **42,90 km2** **YAKLAŞIK KOT : 584 m**

GÖZLEM SÜRESİ : **01.08.1991 - 30.09.2006**

ORTALAMA AKIMLAR : **Gözlem süresinde 0.079 m3/sn. (15 Yıllık) 2006 Su yılında 0.043 m3/sn.**

ANLIK EN ÇOK VE EN AZ AKIMLAR:

2006 Su yılında anlık ençok akım	**:**	**1.22**	**m3/sn**	**01.03.2006**
2006 Su yılında anlık enaz akım	**:**	**0.003**	**m3/sn**	**04.02.2006**
Gözlem süresinde anlık ençok akım	**:**	**11.7**	**m3/sn**	**19.07.2002**
Gözlem süresinde anlık enaz akım	**:**	**0.000**	**m3/sn**	**06.07.1994**

7. Anahtar Eğrisi (Seviyeler cm olarak)

Seviye	Akım	Seviye	Akım	Seviye	Akım	Seviye	Akım
20	0.000	38	0.090	48	0.440	90	4.2
22	0.001	40	0.160	50	0.540	100	5.5
28	0.008	42	0.210	55	0.930	120	8.6
31	0.022	44	0.280	60	1.2	140	12.5
35	0.060	46	0.350	75	2.5	150	14.7

Akımlar 01 Ekim 2005 'den 30 Eylül 2006' a kadar m3/sn olarak

Gün	Ekim	Kasım	Aralık	Ocak	Şubat	Mart	Nisan	Mayıs	Haziran	Temmuz	Ağustos	Eylül
01	0.012	0.022	0.070	0.031	0.070	0.440	0.049	0.022	0.022	0.012	0.006	0.006
02	0.008	0.022	0.070	0.031	0.049	0.696	0.049	0.022	0.016	0.012	0.008	0.012
03	0.012	0.022	0.070	0.031	0.031	0.618	0.031	0.022	0.012	0.012	0.008	0.012
04	0.012	0.040	0.070	0.031	0.016	0.490	0.049	0.022	0.012	0.008	0.006	0.008
05	0.012	0.070	0.070	0.031	0.016	0.350	0.070	0.022	0.012	0.008	0.005	0.008
06	0.012	0.060	0.070	0.031	0.022	0.350	0.070	0.016	0.012	0.008	0.005	0.008
07	0.012	0.040	0.070	0.031	0.049	0.280	0.060	0.022	0.008	0.008	0.005	0.008
08	0.012	0.040	0.040	0.031	0.040	0.210	0.031	0.060	0.008	0.008	0.005	0.008
09	0.012	0.040	0.022	0.031	0.049	0.210	0.031	0.060	0.012	0.008	0.005	0.008
10	0.012	0.031	0.022	0.031	0.049	0.245	0.031	0.040	0.016	0.008	0.005	0.008
11	0.016	0.031	0.022	0.031	0.060	0.210	0.031	0.031	0.016	0.008	0.005	0.008
12	0.012	0.031	0.022	0.031	0.060	0.160	0.022	0.031	0.016	0.008	0.005	0.008
13	0.012	0.031	0.022	0.031	0.060	0.160	0.022	0.049	0.016	0.008	0.005	0.008
14	0.012	0.031	0.022	0.031	0.060	0.160	0.022	0.080	0.031	0.008	0.005	0.008
15	0.012	0.031	0.022	0.031	0.049	0.160	0.022	0.070	0.022	0.012	0.005	0.008
16	0.016	0.022	0.022	0.031	0.049	0.070	0.022	0.049	0.022	0.008	0.005	0.008
17	0.022	0.031	0.022	0.040	0.049	0.060	0.022	0.049	0.016	0.008	0.005	0.008
18	0.022	0.031	0.022	0.022	0.060	0.060	0.022	0.049	0.016	0.012	0.005	0.008
19	0.016	0.031	0.022	0.031	0.060	0.060	0.022	0.040	0.016	0.012	0.005	0.008
20	0.031	0.031	0.031	0.031	0.070	0.060	0.022	0.031	0.012	0.012	0.005	0.012
21	0.031	0.080	0.022	0.031	0.090	0.049	0.022	0.031	0.012	0.012	0.005	0.012
22	0.022	0.090	0.031	0.031	0.185	0.049	0.031	0.031	0.012	0.012	0.005	0.016
23	0.022	0.080	0.022	0.040	0.185	0.049	0.031	0.022	0.012	0.008	0.005	0.016
24	0.022	0.070	0.022	0.049	0.185	0.049	0.031	0.022	0.012	0.006	0.005	0.016
25	0.016	0.070	0.031	0.049	0.185	0.049	0.031	0.022	0.012	0.006	0.006	0.016
26	0.016	0.070	0.022	0.049	0.280	0.049	0.031	0.022	0.012	0.006	0.006	0.022
27	0.016	0.070	0.031	0.049	0.395	0.049	0.022	0.022	0.012	0.006	0.006	0.016
28	0.016	0.070	0.031	0.049	0.395	0.049	0.022	0.022	0.012	0.006	0.006	0.016
29	0.016	0.070	0.031	0.049	-----	0.049	0.022	0.022	0.012	0.006	0.006	0.016
30	0.022	0.070	0.031	0.060	-----	0.049	0.022	0.022	0.012	0.006	0.006	0.016
31	0.022	-----	0.031	0.070	-----	0.049	-----	0.022	-----	0.006	0.006	-----
Maks.	0.049	0.090	0.080	0.125	0.440	1.22	0.070	0.080	0.031	0.016	0.040	0.022
Min.	0.008	0.022	0.006	0.022	0.003	0.049	0.022	0.016	0.008	0.006	0.003	0.006
Ortalama	0.016	0.048	0.036	0.037	0.102	0.180	0.032	0.034	0.014	0.009	0.005	0.011
LT/SN/Km2	0.382	1.11	0.833	0.862	2.39	4.20	0.750	0.787	0.336	0.202	0.128	0.258
AKIM mm.	1.02	2.88	2.23	2.31	5.78	11.3	1.94	2.11	0.872	0.540	0.342	0.669
MİL. M3	0.044	0.123	0.096	0.099	0.248	0.483	0.083	0.090	0.037	0.023	0.015	0.029

SU YILI (2006) YILLIK TOPLAM AKIM 1.37 MİLYON M3 32 MM. 1.0 LT/SN/Km2

15. Kizilirmak Havzasi

D15A260 KUTANÖZÜ DERESİ ŞARKIŞLA

YERİ : **SİVAS ŞARKIŞLA İLÇESİ KUTAN MEVKİNDEDİR**
36°28'4" Doğu - 39°16'40" Kuzey

YAĞIŞ ALANI : **68,00 km2** **YAKLAŞIK KOT : 1280 m**

GÖZLEM SÜRESİ : **01.10.1993 - 30.09.2006**

ORTALAMA AKIMLAR : **Gözlem süresinde 0.174 m3/sn. (12 Yıllık) 2006 Su yılında 0.135 m3/sn.**

ANLIK EN ÇOK VE EN AZ AKIMLAR:

2006 Su yılında anlık ençok akım	**:**	**63.4**	**m3/sn**	**28.06.2006**
2006 Su yılında anlık enaz akım	**:**	**0.000**	**m3/sn**	**01.10.2005**
Gözlem süresinde anlık ençok akım	**:**	**77.0**	**m3/sn**	**02.08.1998**
Gözlem süresinde anlık enaz akım	**:**	**0.000**	**m3/sn**	**01.08.1994**

Akımlar 01 Ekim 2005 'den 30 Eylül 2006' a kadar m3/sn olarak

Gün	Ekim	Kasım	Aralık	Ocak	Şubat	Mart	Nisan	Mayıs	Haziran	Temmuz	Ağustos	Eylül
01	KURU	KURU	KURU	KURU	KURU	0.084	0.220	0.390	0.390	0.173	0.049	0.018
02	KURU	KURU	KURU	KURU	KURU	0.125	0.474	0.726	0.290	0.173	0.049	0.018
03	0.011	KURU	KURU	KURU	KURU	0.220	0.642	0.948	0.290	0.173	0.049	0.018
04	0.001	KURU	KURU	KURU	KURU	0.558	0.558	0.642	0.290	0.200	0.049	0.018
05	KURU	KURU	KURU	KURU	KURU	0.390	0.474	0.642	0.290	0.235	0.049	0.018
06	KURU	KURU	KURU	KURU	KURU	0.390	0.390	0.558	0.220	0.235	0.049	0.018
07	KURU	KURU	KURU	KURU	KURU	0.474	0.390	0.390	0.170	0.200	0.049	0.018
08	KURU	KURU	KURU	KURU	KURU	0.726	0.290	0.390	0.170	0.147	0.037	0.018
09	KURU	KURU	KURU	KURU	KURU	0.558	0.290	0.390	0.170	0.122	0.037	0.018
10	KURU	KURU	KURU	KURU	KURU	0.390	0.290	0.390	0.170	0.122	0.037	0.018
11	KURU	KURU	KURU	KURU	KURU	0.290	0.290	0.390	0.170	0.100	0.037	0.018
12	KURU	KURU	KURU	KURU	KURU	0.290	0.290	0.390	0.170	0.081	0.037	0.018
13	KURU	KURU	KURU	KURU	KURU	0.290	0.220	0.390	0.170	0.081	0.037	0.018
14	KURU	KURU	KURU	KURU	0.001	0.290	0.220	0.290	0.170	0.064	0.037	0.018
15	KURU	KURU	KURU	KURU	0.004	0.290	0.220	0.474	0.170	0.064	0.037	KURU
16	KURU	KURU	KURU	KURU	0.011	0.290	0.220	0.726	0.125	0.064	0.037	KURU
17	KURU	KURU	KURU	KURU	0.011	0.290	0.220	0.726	0.125	0.049	0.037	KURU
18	KURU	KURU	KURU	KURU	0.021	0.290	0.170	0.726	0.125	0.049	0.037	KURU
19	KURU	KURU	KURU	KURU	0.021	0.290	0.125	0.726	0.084	0.049	0.037	KURU
20	KURU	KURU	KURU	KURU	0.021	0.290	0.125	0.642	0.084	0.049	0.037	KURU
21	KURU	KURU	KURU	KURU	0.021	0.290	0.125	0.726	0.084	0.049	0.037	KURU
22	KURU	KURU	KURU	KURU	0.021	0.474	0.125	0.810	0.054	0.049	0.037	KURU
23	KURU	KURU	KURU	KURU	0.021	0.390	0.290	0.726	0.034	0.049	0.037	KURU
24	KURU	KURU	KURU	KURU	0.034	0.220	0.474	0.642	0.034	0.049	0.026	KURU
25	KURU	KURU	KURU	KURU	0.034	0.474	0.474	0.558	0.034	0.049	0.026	KURU
26	KURU	KURU	KURU	KURU	0.034	0.474	0.290	0.558	0.034	0.049	0.018	KURU
27	KURU	KURU	KURU	KURU	0.054	0.390	0.220	0.810	0.034	0.049	0.018	KURU
28	KURU	KURU	KURU	KURU	0.054	0.390	0.170	0.642	1.95	0.049	0.018	KURU
29	KURU	KURU	KURU	KURU	-----	0.290	0.170	0.474	0.944	0.049	0.018	KURU
30	KURU	KURU	KURU	KURU	-----	0.220	0.474	0.474	0.173	0.049	0.018	KURU
31	KURU	-----	KURU	KURU	-----	0.220	-----	0.390	-----	0.049	0.018	-----
Maks.	3.44	KURU	KURU	KURU	0.084	1.22	7.51	3.61	63.4	0.235	0.049	0.018
Min.	KURU	KURU	KURU	KURU	KURU	0.084	0.054	0.220	0.034	0.049	0.018	KURU
Ortalama	0.000	KURU	KURU	KURU	0.013	0.343	0.298	0.573	0.241	0.096	0.035	0.008
LT/SN/Km2	0.006	0.000	0.000	0.000	0.191	5.05	4.38	8.42	3.54	1.41	0.519	0.124
AKIM mm.	0.015	0.000	0.000	0.000	0.461	13.5	11.3	22.6	9.17	3.77	1.39	0.320
MİL. M3	0.001	0.000	0.000	0.000	0.031	0.920	0.772	1.53	0.624	0.257	0.095	0.022

SU YILI (2006) YILLIK TOPLAM AKIM 4.25 MİLYON M3 63 MM. 2.0 LT/SN/Km2

15. Kizilirmak Havzasi

D15A261 DUMANLI ÇAYI OLUKMAN

YERİ : **SİVAS MERKEZ OLUKMAN KÖYÜ GİRİŞİNDEDİR**
36°58'15" Doğu - 40°0'48" Kuzey

YAĞIŞ ALANI : **254,90 km2** **YAKLAŞIK KOT : 1374 m**

GÖZLEM SÜRESİ : **01.10.1993 - 30.09.2006**

ORTALAMA AKIMLAR : **Gözlem süresinde 2.393 m3/sn. (13 Yıllık) 2006 Su yılında 2.551 m3/sn.**

ANLIK EN ÇOK VE EN AZ AKIMLAR:

2006 Su yılında anlık ençok akım	:	**43.5**	**m3/sn**	**25.03.2006**
2006 Su yılında anlık enaz akım	:	**0.154**	**m3/sn**	**06.08.2006**
Gözlem süresinde anlık ençok akım	:	**112.**	**m3/sn**	**05.03.2004**
Gözlem süresinde anlık enaz akım	:	**0.000**	**m3/sn**	**25.07.1999**

Akımlar 01 Ekim 2005 'den 30 Eylül 2006' a kadar m3/sn olarak

Gün	Ekim	Kasım	Aralık	Ocak	Şubat	Mart	Nisan	Mayıs	Haziran	Temmuz	Ağustos	Eylül
01	0.245	0.315	1.45	1.08	0.838	7.41	11.1	7.41	1.45	0.315	0.210	0.175
02	0.245	0.315	1.36	1.08	0.838	7.66	14.4	6.92	1.36	0.280	0.210	0.175
03	0.245	0.315	1.36	1.08	0.914	11.1	12.0	5.94	1.27	0.280	0.210	0.175
04	0.245	0.315	1.27	1.08	0.914	11.1	9.72	5.04	1.08	0.280	0.210	0.175
05	0.210	0.402	1.17	1.08	0.838	9.20	9.72	6.68	0.914	0.280	0.210	0.175
06	0.210	0.402	1.17	1.08	0.990	11.1	9.20	9.46	0.838	0.280	0.175	0.175
07	0.210	0.506	1.08	1.17	1.17	15.0	9.20	9.98	0.762	0.315	0.175	0.175
08	0.210	0.506	1.08	1.17	1.78	26.2	10.5	11.4	0.762	0.315	0.175	0.175
09	0.210	0.558	1.08	1.08	2.00	15.9	12.6	8.42	0.762	0.315	0.175	0.175
10	0.245	0.558	0.990	1.08	1.67	10.8	12.3	7.17	0.686	0.280	0.175	0.175
11	0.245	0.558	0.914	0.990	1.89	8.16	14.1	5.94	0.686	0.280	0.175	0.175
12	0.245	0.558	0.914	1.08	2.80	9.98	10.8	5.04	0.686	0.280	0.175	0.175
13	0.245	0.506	0.838	0.990	2.80	8.16	9.46	5.04	0.610	0.280	0.175	0.175
14	0.245	0.506	0.838	0.990	2.52	9.98	8.42	4.63	0.610	0.280	0.175	0.175
15	0.245	0.506	0.838	0.838	2.13	9.72	8.68	4.02	0.610	0.245	0.210	0.175
16	0.245	0.506	0.990	0.686	1.78	8.42	8.68	4.43	0.558	0.210	0.210	0.175
17	0.245	0.506	1.08	0.762	1.78	7.66	6.68	9.46	0.558	0.210	0.175	0.175
18	0.245	0.506	1.08	0.762	1.89	6.68	5.45	5.70	0.506	0.210	0.210	0.175
19	0.762	0.610	2.80	0.838	1.89	6.68	4.84	4.84	0.454	0.210	0.210	0.175
20	0.350	0.686	2.80	0.686	1.89	5.70	4.63	4.22	0.454	0.210	0.175	0.175
21	0.506	0.990	2.13	0.838	1.89	5.45	4.22	3.61	0.454	0.210	0.175	0.175
22	0.454	1.56	1.78	0.838	2.00	6.92	3.81	3.25	0.454	0.210	0.175	0.210
23	0.350	1.36	1.67	0.914	2.26	7.17	3.61	2.95	0.402	0.210	0.175	0.210
24	0.350	1.36	1.45	0.838	2.52	9.20	3.61	2.65	0.402	0.210	0.175	0.210
25	0.315	1.36	1.36	0.914	3.10	27.6	4.22	2.39	0.402	0.210	0.175	0.210
26	0.315	1.36	1.36	0.914	4.43	18.5	3.40	2.26	0.402	0.210	0.175	0.210
27	0.315	1.36	1.17	0.838	5.70	13.2	2.95	3.81	0.350	0.210	0.175	0.210
28	0.315	1.45	1.27	0.838	5.94	10.8	2.95	2.95	0.315	0.210	0.175	0.210
29	0.315	1.45	1.08	0.838	-----	9.72	3.61	2.39	0.315	0.210	0.175	0.175
30	0.315	1.56	1.08	0.838	-----	9.98	7.66	1.89	0.315	0.210	0.175	0.175
31	0.315	-----	1.17	0.838	-----	10.2	-----	1.56	-----	0.210	0.175	-----
Maks.	2.95	1.56	5.25	1.17	8.16	43.5	16.8	26.2	1.67	0.350	0.210	0.210
Min.	0.210	0.315	0.762	0.558	0.762	5.04	2.65	1.45	0.315	0.210	0.154	0.175
Ortalama	0.297	0.782	1.31	0.937	2.18	10.8	7.75	5.21	0.648	0.247	0.185	0.183
LT/SN/Km2	1.17	3.07	5.14	3.68	8.57	42.4	30.4	20.4	2.54	0.970	0.726	0.719
AKIM mm.	3.12	7.95	13.8	9.85	20.7	114.	78.8	54.7	6.58	2.60	1.95	1.86
MİL. M3	0.796	2.03	3.51	2.51	5.28	29.0	20.1	13.9	1.68	0.662	0.496	0.475

SU YILI (2006) YILLIK TOPLAM AKIM 80.44 MİLYON M3 316 MM. 10.0 LT/SN/Km2

15. Kizilirmak Havzasi

D15A262 GÖK DERE KURTLAPA

YERİ : **SİVAS MERKEZ KURTLAPA BELDESİ GİRİŞİNİN DOĞUSUNDADIR**
37°2'41" Doğu - 40°3'58" Kuzey

YAĞIŞ ALANI : **47,90 km2** **YAKLAŞIK KOT : 1420 m**

GÖZLEM SÜRESİ : **01.10.1993 - 30.09.2006**

ORTALAMA AKIMLAR : **Gözlem süresinde 0.389 m3/sn. (10 Yıllık) 2006 Su yılında 0.340 m3/sn.**

ANLIK EN ÇOK VE EN AZ AKIMLAR:

2006 Su yılında anlık ençok akım	**:**	**4.45**	**m3/sn**	**25.03.2006**
2006 Su yılında anlık enaz akım	**:**	**0.000**	**m3/sn**	**01.10.2005**
Gözlem süresinde anlık ençok akım	**:**	**8.15**	**m3/sn**	**27.03.1994**
Gözlem süresinde anlık enaz akım	**:**	**0.000**	**m3/sn**	**01.08.1994**

Akımlar 01 Ekim 2005 'den 30 Eylül 2006' a kadar m3/sn olarak

Gün	Ekim	Kasım	Aralık	Ocak	Şubat	Mart	Nisan	Mayıs	Haziran	Temmuz	Ağustos	Eylül
01	KURU	0.045	0.185	0.115	0.020	0.980	1.91	0.980	0.265	0.013	0.001	KURU
02	KURU	0.045	0.150	0.115	0.020	0.980	2.55	0.980	0.215	0.013	0.001	KURU
03	KURU	0.045	0.150	0.115	0.020	1.67	2.07	0.836	0.215	0.013	0.001	KURU
04	KURU	0.045	0.115	0.115	0.020	1.83	1.75	0.620	0.185	0.020	0.001	KURU
05	KURU	0.086	0.115	0.115	0.020	1.51	1.59	0.908	0.150	0.020	KURU	KURU
06	KURU	0.086	0.086	0.115	0.020	1.83	1.43	1.35	0.115	0.020	KURU	KURU
07	KURU	0.086	0.086	0.115	0.115	2.35	1.35	1.43	0.115	0.020	KURU	KURU
08	KURU	0.065	0.086	0.115	0.215	3.46	1.43	1.67	0.115	0.020	KURU	KURU
09	KURU	0.065	0.086	0.115	0.265	2.45	1.51	1.28	0.086	0.020	KURU	KURU
10	KURU	0.065	0.086	0.115	0.265	1.67	1.35	1.05	0.086	0.020	KURU	KURU
11	KURU	0.045	0.086	0.086	0.265	1.28	1.51	0.836	0.086	0.013	KURU	KURU
12	KURU	0.045	0.086	0.086	0.265	1.20	0.980	0.692	0.065	0.013	KURU	KURU
13	KURU	0.045	0.065	0.086	0.355	1.43	0.836	0.620	0.065	0.013	KURU	KURU
14	KURU	0.045	0.065	0.086	0.310	1.67	0.764	0.567	0.086	0.008	KURU	KURU
15	KURU	0.045	0.065	0.086	0.215	1.51	0.764	0.461	0.065	0.013	KURU	KURU
16	KURU	0.045	0.086	0.185	0.185	1.51	0.692	0.620	0.065	0.013	KURU	KURU
17	0.008	0.045	0.115	0.265	0.013	1.35	0.567	1.43	0.065	0.008	KURU	KURU
18	0.020	0.045	0.150	0.115	0.013	1.13	0.461	0.836	0.065	0.008	KURU	KURU
19	0.215	0.065	0.620	0.086	0.013	1.13	0.461	0.692	0.045	0.008	KURU	KURU
20	0.115	0.065	0.461	0.065	0.150	0.980	0.355	0.567	0.045	0.008	KURU	KURU
21	0.185	0.185	0.355	0.065	0.185	0.836	0.355	0.461	0.030	0.008	KURU	KURU
22	0.150	0.310	0.265	0.065	0.215	1.28	0.355	0.408	0.030	0.008	KURU	KURU
23	0.115	0.215	0.265	0.065	0.265	1.28	0.310	0.355	0.030	0.008	KURU	KURU
24	0.086	0.215	0.215	0.065	0.265	1.67	0.408	0.310	0.020	0.008	KURU	KURU
25	0.065	0.185	0.185	0.065	0.310	3.55	0.567	0.265	0.013	0.008	KURU	KURU
26	0.045	0.185	0.150	0.065	0.514	2.74	0.461	0.215	0.013	0.005	KURU	KURU
27	0.045	0.185	0.115	0.065	0.692	2.07	0.408	0.461	0.013	0.005	KURU	KURU
28	0.045	0.185	0.185	0.065	0.764	1.75	0.355	0.355	0.020	0.005	KURU	KURU
29	0.045	0.185	0.115	0.065	-----	1.51	0.461	0.265	0.020	0.005	KURU	KURU
30	0.045	0.185	0.115	0.020	-----	1.59	0.980	0.265	0.013	0.002	KURU	KURU
31	0.045	-----	0.115	0.020	-----	1.67	-----	0.265	-----	0.002	KURU	-----
Maks.	1.13	0.355	0.692	1.20	1.13	4.45	3.28	4.18	0.265	0.086	0.005	KURU
Min.	KURU	0.045	0.065	0.020	0.013	0.764	0.310	0.215	0.013	0.002	KURU	KURU
Ortalama	0.040	0.105	0.162	0.094	0.213	1.67	0.966	0.711	0.080	0.011	0.000	KURU
LT/SN/Km2	0.828	2.20	3.38	1.97	4.45	34.9	20.2	14.8	1.67	0.234	0.003	0.000
AKIM mm.	2.22	5.70	9.06	5.27	10.8	93.6	52.3	39.8	4.33	0.628	0.007	0.000
MİL. M3	0.106	0.273	0.434	0.252	0.516	4.48	2.50	1.91	0.207	0.030	0.000	0.000

SU YILI (2006) YILLIK TOPLAM AKIM 10.71 MİLYON M3 224 MM. 7.1 LT/SN/Km2

15. Kizilirmak Havzasi

D15A264 KIRIKÖZÜ D. ÇUKUR

YERİ : **ÖZVATAN İLÇESİNDEN TAŞCI KÖYÜ İSTİKAMETİNE GİDEN YOLUN4.KM SİNDE YOLUN SAĞINDA 100 M MESAFEDEDİR.**
35°45'4" Doğu - 39°7'39" Kuzey

YAĞIŞ ALANI : **91,00 km2** **YAKLAŞIK KOT : 1380 m**

GÖZLEM SÜRESİ : **01.10.1993 - 30.09.2006**

ORTALAMA AKIMLAR : **Gözlem süresinde 0.090 m3/sn. (11 Yıllık) 2006 Su yılında 0.004 m3/sn.**

ANLIK EN ÇOK VE EN AZ AKIMLAR:

2006 Su yılında anlık ençok akım	**:**	**0.088 m3/sn**	**24.04.2006**
2006 Su yılında anlık enaz akım	**:**	**0.000 m3/sn**	**01.10.2005**
Gözlem süresinde anlık ençok akım	**:**	**1.13 m3/sn**	**22.05.1998**
Gözlem süresinde anlık enaz akım	**:**	**0.000 m3/sn**	**10.05.1995**

İstasyon için kullanılmış anahtar bulunamadı.

Akımlar 01 Ekim 2005 'den 30 Eylül 2006' a kadar m3/sn olarak

Gün	Ekim	Kasım	Aralık	Ocak	Şubat	Mart	Nisan	Mayıs	Haziran	Temmuz	Ağustos	Eylül
01	KURU	KURU	KURU	KURU	KURU	KURU	0.015	0.033	0.015	KURU	KURU	KURU
02	KURU	KURU	KURU	KURU	KURU	KURU	0.022	0.033	0.015	KURU	KURU	KURU
03	KURU	KURU	KURU	KURU	KURU	KURU	0.022	0.033	0.015	KURU	KURU	KURU
04	KURU	KURU	KURU	KURU	KURU	KURU	0.022	0.033	0.015	KURU	KURU	KURU
05	KURU	KURU	KURU	KURU	KURU	KURU	0.015	0.033	0.003	KURU	KURU	KURU
06	KURU	KURU	KURU	KURU	KURU	KURU	0.015	0.033	0.003	KURU	KURU	KURU
07	KURU	KURU	KURU	KURU	KURU	KURU	0.022	0.033	0.005	KURU	KURU	KURU
08	KURU	KURU	KURU	KURU	KURU	KURU	0.022	0.033	0.005	KURU	KURU	KURU
09	KURU	KURU	KURU	KURU	KURU	KURU	0.022	0.033	0.005	KURU	KURU	KURU
10	KURU	KURU	KURU	KURU	KURU	KURU	0.015	0.022	0.005	KURU	KURU	KURU
11	KURU	KURU	KURU	KURU	KURU	KURU	0.015	0.022	0.005	KURU	KURU	KURU
12	KURU	KURU	KURU	KURU	KURU	KURU	0.015	0.022	0.005	KURU	KURU	KURU
13	KURU	KURU	KURU	KURU	KURU	KURU	0.010	0.022	0.005	KURU	KURU	KURU
14	KURU	KURU	KURU	KURU	KURU	KURU	0.010	0.022	0.005	KURU	KURU	KURU
15	KURU	KURU	KURU	KURU	KURU	KURU	0.010	0.022	0.005	KURU	KURU	KURU
16	KURU	KURU	KURU	KURU	KURU	KURU	0.010	0.022	0.005	KURU	KURU	KURU
17	KURU	KURU	KURU	KURU	KURU	KURU	0.007	0.022	0.005	KURU	KURU	KURU
18	KURU	KURU	KURU	KURU	KURU	KURU	0.007	0.022	0.005	KURU	KURU	KURU
19	KURU	KURU	KURU	KURU	KURU	KURU	0.007	0.022	0.005	KURU	KURU	KURU
20	KURU	KURU	KURU	KURU	KURU	KURU	0.007	0.022	0.005	KURU	KURU	KURU
21	KURU	KURU	KURU	KURU	KURU	KURU	0.007	0.022	0.005	KURU	KURU	KURU
22	KURU	KURU	KURU	KURU	KURU	KURU	0.007	0.015	0.005	KURU	KURU	KURU
23	KURU	KURU	KURU	KURU	KURU	0.007	0.010	0.015	0.005	KURU	KURU	KURU
24	KURU	KURU	KURU	KURU	KURU	0.007	0.065	0.015	KURU	KURU	KURU	KURU
25	KURU	KURU	KURU	KURU	KURU	0.007	0.033	0.015	KURU	KURU	KURU	KURU
26	KURU	KURU	KURU	KURU	KURU	0.010	0.033	0.015	KURU	KURU	KURU	KURU
27	KURU	KURU	KURU	KURU	KURU	0.010	0.033	0.015	KURU	KURU	KURU	KURU
28	KURU	KURU	KURU	KURU	KURU	0.015	0.033	0.015	KURU	KURU	KURU	KURU
29	KURU	KURU	KURU	KURU	-----	0.015	0.022	0.015	KURU	KURU	KURU	KURU
30	KURU	KURU	KURU	KURU	-----	0.015	0.022	0.015	KURU	KURU	KURU	KURU
31	KURU	-----	KURU	KURU	-----	0.015	-----	0.015	-----	KURU	KURU	-----
Maks.	KURU	KURU	KURU	KURU	KURU	0.015	0.088	0.033	0.015	KURU	KURU	KURU
Min.	KURU	KURU	KURU	KURU	KURU	KURU	0.007	0.015	KURU	KURU	KURU	KURU
Ortalama	KURU	KURU	KURU	KURU	KURU	0.003	0.019	0.023	0.005	KURU	KURU	KURU
LT/SN/Km2	0.000	0.000	0.000	0.000	0.000	0.036	0.203	0.252	0.055	0.000	0.000	0.000
AKIM mm.	0.000	0.000	0.000	0.000	0.000	0.096	0.527	0.675	0.143	0.000	0.000	0.000
MİL. M3	0.000	0.000	0.000	0.000	0.000	0.009	0.048	0.061	0.013	0.000	0.000	0.000

SU YILI (2006) YILLIK TOPLAM AKIM 0.13 MİLYON M3 1 MM. 0.0 LT/SN/Km2

15. Kizilirmak Havzasi

D15A265 GEÇMİS DERE YUSUFOGLAN

YERİ : **SİVAS YILDIZELİ İLÇESİ YUSUFOĞLAN KÖYÜ ÇIKIŞINDADIR**
36°54'15" Doğu - 40°9'12" Kuzey

YAĞIŞ ALANI : **35,50 km2** **YAKLAŞIK KOT : 1400 m**

GÖZLEM SÜRESİ : **01.01.1996 - 30.09.2006**

ORTALAMA AKIMLAR : **Gözlem süresinde 0.463 m3/sn. (10 Yıllık) 2006 Su yılında 0.493 m3/sn.**

ANLIK EN ÇOK VE EN AZ AKIMLAR:

2006 Su yılında anlık ençok akım	:	**9.49**	**m3/sn**	**25.03.2006**
2006 Su yılında anlık enaz akım	:	**0.040**	**m3/sn**	**01.10.2005**
Gözlem süresinde anlık ençok akım	:	**27.9**	**m3/sn**	**05.03.2004**
Gözlem süresinde anlık enaz akım	:	**0.001**	**m3/sn**	**13.10.1996**

Akımlar 01 Ekim 2005 'den 30 Eylül 2006' a kadar m3/sn olarak

Gün	Ekim	Kasım	Aralık	Ocak	Şubat	Mart	Nisan	Mayıs	Haziran	Temmuz	Ağustos	Eylül
01	0.040	0.100	0.215	0.242	0.215	0.270	2.18	2.25	0.395	0.190	0.215	0.140
02	0.040	0.118	0.215	0.242	0.215	0.270	2.45	1.95	0.370	0.190	0.215	0.140
03	0.040	0.118	0.215	0.242	0.215	0.270	1.92	1.57	0.335	0.190	0.215	0.215
04	0.040	0.118	0.215	0.242	0.215	0.270	1.53	1.31	0.335	0.190	0.215	0.242
05	0.040	0.140	0.215	0.242	0.215	0.305	1.60	1.44	0.335	0.190	0.215	0.242
06	0.040	0.100	0.215	0.242	0.215	0.305	1.68	1.38	0.305	0.190	0.215	0.242
07	0.040	0.052	0.215	0.242	0.242	0.305	1.76	1.38	0.270	0.215	0.215	0.242
08	0.040	0.052	0.215	0.242	0.242	0.370	2.45	1.80	0.242	0.190	0.215	0.242
09	0.040	0.040	0.215	0.242	0.242	2.36	3.03	1.38	0.242	0.190	0.215	0.242
10	0.040	0.118	0.215	0.242	0.242	1.60	3.03	1.25	0.242	0.190	0.215	0.242
11	0.040	0.215	0.215	0.242	0.242	1.12	3.53	1.06	0.242	0.190	0.215	0.242
12	0.040	0.215	0.215	0.242	0.242	0.992	2.45	0.940	0.242	0.190	0.215	0.242
13	0.052	0.215	0.215	0.242	0.242	1.24	2.09	1.19	0.242	0.190	0.215	0.242
14	0.066	0.215	0.215	0.242	0.242	1.92	1.92	1.13	0.242	0.190	0.215	0.242
15	0.066	0.215	0.215	0.242	0.242	2.09	2.00	0.890	0.242	0.190	0.215	0.215
16	0.066	0.215	0.215	0.242	0.242	1.38	2.18	0.830	0.242	0.190	0.215	0.215
17	0.066	0.215	0.215	0.242	0.242	1.18	1.46	1.65	0.242	0.190	0.215	0.215
18	0.082	0.215	0.215	0.242	0.242	0.992	1.12	1.25	0.242	0.158	0.215	0.190
19	0.082	0.215	0.242	0.242	0.242	0.930	0.930	1.06	0.242	0.158	0.215	0.190
20	0.082	0.215	0.242	0.242	0.242	0.830	0.992	0.890	0.242	0.158	0.215	0.190
21	0.100	0.215	0.242	0.242	0.242	0.780	0.880	0.780	0.242	0.158	0.190	0.215
22	0.100	0.215	0.242	0.242	0.242	0.880	0.780	0.725	0.242	0.158	0.158	0.215
23	0.100	0.215	0.242	0.242	0.242	1.24	0.730	0.680	0.242	0.158	0.158	0.215
24	0.100	0.215	0.242	0.242	0.242	2.18	0.780	0.595	0.242	0.158	0.158	0.215
25	0.100	0.215	0.242	0.242	0.242	5.78	0.880	0.595	0.242	0.190	0.158	0.215
26	0.100	0.215	0.242	0.242	0.242	3.15	0.730	0.510	0.242	0.190	0.158	0.215
27	0.100	0.215	0.215	0.242	0.242	2.00	0.638	1.00	0.215	0.215	0.158	0.215
28	0.100	0.215	0.215	0.242	0.242	1.68	0.680	0.830	0.190	0.215	0.158	0.215
29	0.100	0.215	0.215	0.242	-----	1.60	0.780	0.595	0.190	0.215	0.158	0.242
30	0.100	0.215	0.215	0.215	-----	1.84	1.92	0.510	0.190	0.215	0.140	0.270
31	0.100	-----	0.215	0.215	-----	2.18	-----	0.430	-----	0.215	0.140	-----
Maks.	0.100	0.215	0.242	0.242	0.242	9.49	4.30	2.75	0.395	0.242	0.215	0.270
Min.	0.040	0.040	0.215	0.158	0.215	0.242	0.596	0.395	0.190	0.158	0.140	0.140
Ortalama	0.069	0.175	0.222	0.240	0.236	1.36	1.64	1.09	0.258	0.188	0.195	0.220
LT/SN/Km2	1.95	4.94	6.25	6.77	6.65	38.4	46.1	30.8	7.26	5.28	5.48	6.20
AKIM mm.	5.21	12.8	16.7	18.1	16.1	103.	119.	82.4	18.8	14.2	14.7	16.1
MİL. M3	0.185	0.454	0.595	0.644	0.571	3.66	4.24	2.92	0.668	0.503	0.521	0.571

SU YILI (2006) YILLIK TOPLAM AKIM 15.53 MİLYON M3 438 MM. 13.9 LT/SN/Km2

15. Kizilirmak Havzasi

D15A266 OYRAK D. OYRAK

YERİ : KASTAMONU SEYDİLER KARAYOLUNUN 15.KM SINDEKI AKSINIR VE GULAM KÖYLERI ARASINDAN GEÇEN OYRAK DERESI ÜZERINDEDIR.
33°46'34" Doğu - 41°30'30" Kuzey

YAĞIŞ ALANI : 21,60 km2 YAKLAŞIK KOT : 865 m

GÖZLEM SÜRESİ : 01.11.1995 - 30.09.2006

ORTALAMA AKIMLAR : Gözlem süresinde 0.017 m3/sn. (4 Yıllık) 2006 Su yılında 0.013 m3/sn.

ANLIK EN ÇOK VE EN AZ AKIMLAR:

2006 Su yılında anlık ençok akım	:	0.285 m3/sn	01.03.2006
2006 Su yılında anlık enaz akım	:	0.001 m3/sn	23.04.2006
Gözlem süresinde anlık ençok akım	:	0.428 m3/sn	25.12.2001
Gözlem süresinde anlık enaz akım	:	0.000 m3/sn	15.12.2004

Akımlar 01 Ekim 2005 'den 30 Eylül 2006' a kadar m3/sn olarak

Gün	Ekim	Kasım	Aralık	Ocak	Şubat	Mart	Nisan	Mayıs	Haziran	Temmuz	Ağustos	Eylül
01	0.013	0.006	0.030	0.006	0.004	0.180	0.004	0.003	0.006	0.006	0.006	0.004
02	0.013	0.018	0.030	0.006	0.004	0.105	0.003	0.003	0.004	0.006	0.006	0.004
03	0.013	0.018	0.030	0.018	0.004	0.105	0.003	0.003	0.002	0.006	0.006	0.004
04	0.013	0.018	0.030	0.004	0.004	0.068	0.003	0.003	0.003	0.006	0.006	0.004
05	0.013	0.018	0.030	0.004	0.004	0.030	0.003	0.003	0.068	0.006	0.006	0.004
06	0.013	0.018	0.030	0.004	0.004	0.004	0.003	0.003	0.068	0.006	0.006	0.004
07	0.013	0.018	0.030	0.004	0.004	0.002	0.002	0.003	0.068	0.006	0.006	0.004
08	0.013	0.018	0.030	0.004	0.004	0.002	0.002	0.003	0.068	0.006	0.006	0.004
09	0.013	0.030	0.018	0.004	0.004	0.018	0.003	0.003	0.030	0.006	0.006	0.004
10	0.018	0.030	0.030	0.004	0.004	0.006	0.004	0.003	0.018	0.006	0.006	0.004
11	0.018	0.030	0.006	0.004	0.004	0.018	0.003	0.004	0.018	0.006	0.006	0.004
12	0.018	0.030	0.006	0.004	0.004	0.068	0.003	0.018	0.018	0.006	0.006	0.004
13	0.018	0.018	0.006	0.004	0.004	0.105	0.003	0.018	0.018	0.006	0.006	0.004
14	0.018	0.018	0.006	0.004	0.004	0.068	0.003	0.018	0.018	0.006	0.006	0.004
15	0.018	0.018	0.006	0.004	0.004	0.030	0.003	0.006	0.018	0.006	0.006	0.006
16	0.018	0.018	0.006	0.004	0.004	0.030	0.003	0.018	0.018	0.006	0.006	0.018
17	0.018	0.018	0.006	0.004	0.004	0.018	0.003	0.018	0.018	0.018	0.006	0.018
18	0.018	0.018	0.006	0.004	0.004	0.018	0.002	0.018	0.018	0.018	0.006	0.018
19	0.018	0.018	0.006	0.004	0.004	0.030	0.002	0.018	0.018	0.018	0.006	0.018
20	0.018	0.018	0.006	0.004	0.004	0.030	0.002	0.003	0.018	0.018	0.006	0.006
21	0.030	0.018	0.006	0.004	0.004	0.030	0.002	0.006	0.018	0.018	0.006	0.006
22	0.030	0.030	0.006	0.004	0.003	0.030	0.002	0.004	0.018	0.006	0.006	0.006
23	0.030	0.030	0.006	0.004	0.003	0.018	0.001	0.004	0.018	0.018	0.006	0.006
24	0.018	0.030	0.006	0.004	0.003	0.018	0.002	0.003	0.018	0.018	0.006	0.006
25	0.018	0.030	0.006	0.004	0.002	0.018	0.003	0.004	0.018	0.018	0.006	0.006
26	0.030	0.030	0.006	0.004	0.003	0.018	0.003	0.018	0.018	0.006	0.006	0.018
27	0.030	0.030	0.006	0.004	0.004	0.018	0.003	0.018	0.018	0.006	0.006	0.018
28	0.018	0.030	0.006	0.004	0.018	0.018	0.003	0.018	0.018	0.006	0.006	0.018
29	0.006	0.030	0.006	0.004	-----	0.018	0.003	0.018	0.018	0.006	0.006	0.018
30	0.006	0.030	0.006	0.004	-----	0.018	0.003	0.018	0.018	0.006	0.006	0.018
31	0.006	-----	0.006	0.004	-----	0.006	-----	0.018	-----	0.006	0.004	-----
Maks.	0.030	0.030	0.030	0.018	0.250	0.285	0.006	0.018	0.068	0.018	0.006	0.018
Min.	0.004	0.006	0.006	0.003	0.002	0.002	0.001	0.002	0.001	0.004	0.004	0.003
Ortalama	0.017	0.023	0.013	0.005	0.004	0.037	0.003	0.010	0.023	0.009	0.006	0.009
LT/SN/Km2	0.802	1.06	0.618	0.212	0.198	1.71	0.127	0.445	1.07	0.421	0.275	0.401
AKIM mm.	2.15	2.74	1.66	0.568	0.480	4.58	0.328	1.19	2.78	1.13	0.736	1.04
MİL. M3	0.046	0.059	0.036	0.012	0.010	0.099	0.007	0.026	0.060	0.024	0.016	0.022

SU YILI (2006) YILLIK TOPLAM AKIM 0.42 MİLYON M3 19 MM. 0.6 LT/SN/Km2

15. Kizilirmak Havzasi

D15A268 YUSUFOĞLAN DERESİ YUSUFOĞLAN

YERİ : **SİVAS YILDIZELİ İLÇESİ YUSUFOĞLAN KÖYÜ GİRİŞİNDEDİR**
36°51'58" Doğu - 40°9'30" Kuzey

YAĞIŞ ALANI : **15,50 km2** **YAKLAŞIK KOT : 1380 m**

GÖZLEM SÜRESİ : **01.01.1996 - 30.09.2006**

ORTALAMA AKIMLAR : **Gözlem süresinde 0.347 m3/sn. (10 Yıllık) 2006 Su yılında 0.342 m3/sn.**

ANLIK EN ÇOK VE EN AZ AKIMLAR:

2006 Su yılında anlık ençok akım	:	**3.23**	**m3/sn**	**25.03.2006**
2006 Su yılında anlık enaz akım	:	**0.039**	**m3/sn**	**21.08.2006**
Gözlem süresinde anlık ençok akım	:	**6.82**	**m3/sn**	**07.03.2004**
Gözlem süresinde anlık enaz akım	:	**0.018**	**m3/sn**	**26.12.2002**

Akımlar 01 Ekim 2005 'den 30 Eylül 2006' a kadar m3/sn olarak

Gün	Ekim	Kasım	Aralık	Ocak	Şubat	Mart	Nisan	Mayıs	Haziran	Temmuz	Ağustos	Eylül
01	0.121	0.143	0.205	0.143	0.143	1.09	1.09	0.796	0.365	0.121	0.098	0.039
02	0.098	0.143	0.205	0.143	0.143	1.03	1.43	0.796	0.365	0.121	0.098	0.039
03	0.121	0.143	0.205	0.143	0.143	1.29	1.71	0.796	0.365	0.121	0.098	0.039
04	0.143	0.143	0.165	0.143	0.121	1.36	1.50	0.742	0.325	0.121	0.098	0.039
05	0.143	0.143	0.165	0.143	0.121	1.15	1.43	0.796	0.325	0.121	0.098	0.039
06	0.121	0.165	0.165	0.165	0.121	1.36	1.29	0.742	0.285	0.121	0.098	0.039
07	0.121	0.165	0.165	0.165	0.143	1.64	1.22	0.742	0.285	0.121	0.098	0.039
08	0.121	0.165	0.165	0.205	0.245	2.62	1.22	0.850	0.285	0.121	0.098	0.039
09	0.121	0.165	0.165	0.165	0.285	1.71	1.29	0.796	0.285	0.121	0.098	0.039
10	0.121	0.165	0.165	0.165	0.245	1.09	1.29	0.742	0.285	0.121	0.098	0.039
11	0.121	0.165	0.143	0.165	0.325	0.850	1.43	0.688	0.285	0.121	0.098	0.039
12	0.121	0.165	0.143	0.165	0.451	0.688	1.15	0.634	0.285	0.121	0.098	0.039
13	0.121	0.165	0.143	0.165	0.408	0.688	1.03	0.634	0.245	0.121	0.098	0.039
14	0.121	0.165	0.143	0.165	0.365	0.688	0.910	0.580	0.245	0.121	0.098	0.039
15	0.121	0.165	0.143	0.143	0.245	0.850	0.970	0.537	0.245	0.121	0.098	0.039
16	0.121	0.165	0.165	0.143	0.245	0.742	0.910	0.580	0.205	0.098	0.098	0.039
17	0.121	0.165	0.165	0.165	0.325	0.742	0.796	0.742	0.205	0.098	0.098	0.039
18	0.121	0.165	0.165	0.165	0.285	0.688	0.688	0.634	0.205	0.098	0.098	0.039
19	0.143	0.165	0.165	0.165	0.245	0.688	0.580	0.580	0.205	0.098	0.098	0.039
20	0.143	0.165	0.165	0.143	0.245	0.688	0.537	0.537	0.165	0.098	0.098	0.039
21	0.143	0.165	0.165	0.121	0.245	0.634	0.494	0.537	0.165	0.098	0.054	0.039
22	0.143	0.205	0.165	0.143	0.285	0.688	0.494	0.494	0.165	0.098	0.039	0.039
23	0.143	0.165	0.165	0.121	0.325	0.742	0.494	0.494	0.165	0.098	0.039	0.039
24	0.143	0.165	0.165	0.121	0.325	0.850	0.580	0.451	0.165	0.098	0.039	0.039
25	0.143	0.165	0.165	0.121	0.365	2.53	0.742	0.408	0.205	0.098	0.039	0.039
26	0.143	0.165	0.165	0.143	0.580	2.02	0.634	0.365	0.205	0.098	0.039	0.039
27	0.143	0.245	0.165	0.143	0.796	1.57	0.634	0.688	0.143	0.098	0.039	0.039
28	0.143	0.325	0.165	0.143	0.850	1.29	0.634	0.537	0.121	0.098	0.039	0.039
29	0.143	0.325	0.165	0.143	-----	1.15	0.688	0.494	0.121	0.098	0.039	0.039
30	0.143	0.285	0.165	0.143	-----	1.09	0.688	0.494	0.121	0.098	0.039	0.039
31	0.143	-----	0.143	0.143	-----	0.970	-----	0.408	-----	0.098	0.039	-----
Maks.	0.205	0.325	0.245	0.205	1.09	3.23	1.85	1.85	0.365	0.121	0.098	0.054
Min.	0.076	0.143	0.143	0.098	0.121	0.634	0.494	0.365	0.121	0.098	0.039	0.039
Ortalama	0.131	0.180	0.165	0.150	0.308	1.14	0.952	0.623	0.235	0.109	0.078	0.039
LT/SN/Km2	8.45	11.6	10.6	9.68	19.9	73.2	61.4	40.2	15.1	7.04	5.00	2.52
AKIM mm.	22.6	30.1	28.4	25.9	48.0	196.	159.	108.	39.2	18.9	13.4	6.52
MİL. M3	0.351	0.467	0.441	0.402	0.745	3.04	2.47	1.67	0.608	0.292	0.208	0.101

SU YILI (2006) YILLIK TOPLAM AKIM 10.80 MİLYON M3 696 MM. 22.1 LT/SN/Km2

15. Kizilirmak Havzasi

D15A272 KUZUCAĞIN DERE MESTAN

YERİ : **SİVAS ZARA İLÇESİ MESTAN ÇİFTLİĞİ GİRİŞİNDEDİR**
37°42'34" Doğu - 39°56'44" Kuzey

YAĞIŞ ALANI : **111,00 km2** **YAKLAŞIK KOT : 1410 m**

GÖZLEM SÜRESİ : **01.10.1996 - 30.09.2006**

ORTALAMA AKIMLAR : **Gözlem süresinde 1.690 m3/sn. (9 Yıllık) 2006 Su yılında 1.690 m3/sn.**

ANLIK EN ÇOK VE EN AZ AKIMLAR:

2006 Su yılında anlık ençok akım	:	**16.0**	**m3/sn**	**07.05.2006**
2006 Su yılında anlık enaz akım	:	**0.076**	**m3/sn**	**07.02.2006**
Gözlem süresinde anlık ençok akım	:	**54.2**	**m3/sn**	**24.04.2003**
Gözlem süresinde anlık enaz akım	:	**0.076**	**m3/sn**	**07.02.2006**

Akımlar 01 Ekim 2005 'den 30 Eylül 2006' a kadar m3/sn olarak

Gün	Ekim	Kasım	Aralık	Ocak	Şubat	Mart	Nisan	Mayıs	Haziran	Temmuz	Ağustos	Eylül
01	0.264	0.390	0.432	0.432	0.348	1.00	8.30	7.86	2.50	0.558	0.264	0.140
02	0.264	0.432	0.432	0.348	0.348	1.20	9.40	8.52	2.40	0.558	0.264	0.140
03	0.264	0.432	0.432	0.306	0.348	1.60	6.54	7.86	2.30	0.558	0.222	0.140
04	0.348	0.474	0.432	0.306	0.348	1.80	5.47	6.98	2.10	0.516	0.222	0.140
05	0.348	0.558	0.390	0.306	0.348	1.50	5.05	6.76	2.00	0.516	0.222	0.140
06	0.306	0.558	0.390	0.306	0.306	1.90	5.05	6.76	1.90	0.600	0.222	0.140
07	0.306	0.516	0.390	0.348	0.180	2.74	5.47	10.5	1.80	0.600	0.222	0.140
08	0.306	0.474	0.390	0.348	0.222	4.42	6.76	12.0	1.70	0.558	0.180	0.180
09	0.264	0.432	0.348	0.306	0.306	3.58	10.3	9.40	1.50	0.516	0.180	0.180
10	0.222	0.432	0.348	0.264	0.348	2.40	12.0	7.64	1.40	0.474	0.180	0.140
11	0.222	0.390	0.348	0.348	0.306	1.90	11.5	6.76	1.20	0.432	0.180	0.140
12	0.222	0.390	0.348	0.306	0.348	1.70	9.62	6.32	1.10	0.390	0.180	0.140
13	0.222	0.348	0.264	0.306	0.348	1.80	9.62	6.10	1.20	0.390	0.140	0.222
14	0.222	0.348	0.264	0.264	0.348	2.30	9.40	5.68	1.10	0.390	0.140	0.222
15	0.222	0.348	0.306	0.348	0.348	3.72	10.3	5.26	1.10	0.390	0.140	0.222
16	0.264	0.348	0.390	0.348	0.306	2.74	10.1	5.05	1.00	0.390	0.140	0.222
17	0.900	0.348	0.390	0.348	0.390	2.50	8.52	5.26	0.900	0.348	0.140	0.222
18	0.600	0.348	0.348	0.348	0.390	2.10	7.20	4.84	0.800	0.348	0.140	0.222
19	1.00	0.348	0.390	0.348	0.390	1.90	6.32	4.42	0.800	0.348	0.180	0.180
20	0.558	0.348	0.390	0.348	0.390	1.80	6.54	4.00	0.800	0.306	0.222	0.180
21	0.474	0.432	0.348	0.348	0.222	1.60	6.98	4.00	0.800	0.306	0.222	0.180
22	0.432	0.516	0.348	0.348	0.222	1.80	6.54	3.86	0.600	0.306	0.222	0.348
23	0.390	0.390	0.348	0.348	0.474	2.20	6.32	3.86	0.600	0.306	0.222	0.264
24	0.390	0.390	0.306	0.348	0.474	3.16	8.30	3.86	0.600	0.306	0.222	0.264
25	0.390	0.432	0.306	0.348	0.474	10.3	7.64	3.72	0.600	0.306	0.180	0.264
26	0.348	0.432	0.306	0.306	0.600	6.76	5.89	3.58	0.558	0.264	0.180	0.264
27	0.348	0.432	0.390	0.306	0.600	4.63	5.05	3.58	0.558	0.264	0.180	0.264
28	0.306	0.432	0.432	0.348	0.600	4.42	4.42	3.30	0.558	0.264	0.180	0.264
29	0.348	0.432	0.432	0.348	-----	4.21	4.63	3.02	0.600	0.264	0.180	0.264
30	0.348	0.432	0.432	0.348	-----	4.63	10.5	2.74	0.600	0.264	0.180	0.264
31	0.390	-----	0.432	0.348	-----	6.54	-----	2.60	-----	0.264	0.140	-----
Maks.	1.70	0.558	0.432	0.432	1.10	14.5	15.8	16.0	2.50	0.600	0.264	0.390
Min.	0.222	0.306	0.222	0.222	0.076	0.900	4.21	2.50	0.558	0.264	0.140	0.140
Ortalama	0.371	0.419	0.371	0.333	0.369	3.06	7.66	5.68	1.19	0.397	0.190	0.203
LT/SN/Km2	3.34	3.78	3.34	3.00	3.32	27.6	69.0	51.2	10.7	3.57	1.71	1.83
AKIM mm.	8.94	9.79	8.95	8.04	8.04	73.8	179.	137.	27.8	9.57	4.58	4.74
MİL. M3	0.993	1.09	0.994	0.892	0.893	8.20	19.8	15.2	3.08	1.06	0.509	0.526

SU YILI (2006) YILLIK TOPLAM AKIM 53.24 MİLYON M3 480 MM. 15.2 LT/SN/Km2

15. Kizilirmak Havzasi

D15A273 KÖKLÜYURT DERESİ BALTALAR

YERİ : **SİVAS ŞARKIŞLA İLÇESİ BALTALAR KÖYÜNDEDİR**
36°35'46" Doğu - 39°25'5" Kuzey

YAĞIŞ ALANI : **30,00 km2** **YAKLAŞIK KOT : 1365 m**

GÖZLEM SÜRESİ : **01.10.1996 - 30.09.2006**

ORTALAMA AKIMLAR : **Gözlem süresinde 0.096 m3/sn. (10 Yıllık) 2006 Su yılında 0.046 m3/sn.**

ANLIK EN ÇOK VE EN AZ AKIMLAR:

2006 Su yılında anlık ençok akım	**:**	**0.990**	**m3/sn**	**09.05.2006**
2006 Su yılında anlık enaz akım	**:**	**0.000**	**m3/sn**	**01.10.2005**
Gözlem süresinde anlık ençok akım	**:**	**21.9**	**m3/sn**	**11.05.1998**
Gözlem süresinde anlık enaz akım	**:**	**0.000**	**m3/sn**	**23.08.1998**

Akımlar 01 Ekim 2005 'den 30 Eylül 2006' a kadar m3/sn olarak

Gün	Ekim	Kasım	Aralık	Ocak	Şubat	Mart	Nisan	Mayıs	Haziran	Temmuz	Ağustos	Eylül
01	KURU	0.016	0.016	0.016	0.024	0.088	0.110	0.170	0.024	0.012	KURU	KURU
02	KURU	0.016	0.016	0.051	0.024	0.110	0.135	0.270	0.024	0.005	KURU	KURU
03	KURU	0.016	0.016	0.135	0.024	0.135	0.135	0.368	0.024	0.012	KURU	KURU
04	KURU	0.016	0.016	0.110	0.024	0.135	0.110	0.368	0.024	0.005	KURU	KURU
05	KURU	0.016	0.016	0.088	0.024	0.110	0.110	0.310	0.024	0.002	KURU	KURU
06	KURU	0.016	0.016	0.024	0.024	0.110	0.110	0.310	0.024	0.002	KURU	KURU
07	KURU	0.016	0.016	0.024	0.038	0.110	0.110	0.310	0.024	0.003	KURU	KURU
08	KURU	0.016	0.016	0.024	0.068	0.170	0.110	0.310	0.024	0.003	KURU	KURU
09	KURU	0.016	0.016	0.024	0.038	0.170	0.110	0.270	0.024	0.002	KURU	KURU
10	KURU	0.016	0.016	0.024	0.038	0.135	0.068	0.200	0.024	0.002	KURU	KURU
11	KURU	0.016	0.016	0.024	0.068	0.135	0.088	0.170	0.024	0.002	KURU	KURU
12	KURU	0.016	0.016	0.024	0.088	0.110	0.088	0.135	0.024	0.002	KURU	KURU
13	KURU	0.016	0.016	0.024	0.088	0.110	0.088	0.135	0.024	0.002	KURU	KURU
14	KURU	0.016	0.016	0.024	0.051	0.110	0.088	0.170	0.024	0.002	KURU	KURU
15	KURU	0.016	0.016	0.016	0.051	0.110	0.088	0.135	0.016	0.002	KURU	KURU
16	KURU	0.016	0.016	0.024	0.038	0.110	0.088	0.110	0.012	0.002	KURU	KURU
17	KURU	0.016	0.016	0.024	0.016	0.110	0.068	0.110	0.016	0.002	KURU	KURU
18	KURU	0.016	0.016	0.024	0.016	0.110	0.068	0.110	0.001	0.001	KURU	KURU
19	KURU	0.016	0.016	0.024	0.016	0.110	0.068	0.110	KURU	KURU	KURU	KURU
20	KURU	0.016	0.016	0.024	0.005	0.110	0.068	0.110	KURU	KURU	KURU	KURU
21	KURU	0.016	0.016	0.024	0.016	0.135	0.068	0.110	KURU	KURU	KURU	KURU
22	KURU	0.016	0.016	0.024	0.051	0.170	0.068	0.110	KURU	KURU	KURU	KURU
23	KURU	0.016	0.016	0.024	0.051	0.135	0.088	0.110	0.001	KURU	KURU	KURU
24	KURU	0.016	0.016	0.024	0.051	0.135	0.135	0.110	0.002	KURU	KURU	KURU
25	KURU	0.016	0.016	0.024	0.051	0.270	0.235	0.110	0.002	KURU	KURU	KURU
26	KURU	0.016	0.016	0.024	0.068	0.310	0.170	0.088	0.003	KURU	KURU	KURU
27	KURU	0.016	0.016	0.024	0.088	0.235	0.170	0.110	0.002	KURU	KURU	KURU
28	KURU	0.016	0.016	0.024	0.088	0.235	0.135	0.088	0.003	KURU	KURU	KURU
29	KURU	0.016	0.016	0.024	-----	0.235	0.110	0.088	0.003	KURU	KURU	KURU
30	KURU	0.016	0.016	0.024	-----	0.200	0.235	0.068	0.012	KURU	KURU	KURU
31	0.012	-----	0.016	0.024	-----	0.200	-----	0.038	-----	KURU	KURU	-----
Maks.	0.051	0.038	0.038	0.484	0.135	0.678	0.484	0.990	0.024	0.012	KURU	KURU
Min.	KURU	0.016	0.016	0.016	0.002	0.088	0.068	0.038	KURU	KURU	KURU	KURU
Ortalama	0.000	0.016	0.016	0.033	0.044	0.150	0.111	0.168	0.014	0.002	KURU	KURU
LT/SN/Km2	0.013	0.533	0.533	1.09	1.46	5.01	3.69	5.60	0.454	0.068	0.000	0.000
AKIM mm.	0.035	1.38	1.43	2.93	3.53	13.4	9.57	15.0	1.18	0.181	0.000	0.000
MİL. M3	0.001	0.041	0.043	0.088	0.106	0.402	0.287	0.450	0.035	0.005	0.000	0.000

SU YILI (2006) YILLIK TOPLAM AKIM 1.46 MİLYON M3 49 MM. 1.5 LT/SN/Km2

15. Kizilirmak Havzasi

D15A275 PINARBAŞI KAYNAĞI ÇEPNİ

YERİ : **SİVAS GEMEREK İLÇESİ ÇEPNİ BELDESİNDEKİ BALIK ÜRETİM HAVUZLARININ ALTINDADIR**
36°1'40" Doğu - 39°19'37" Kuzey

YAĞIŞ ALANI : **20,10 km2** **YAKLAŞIK KOT : 1345 m**

GÖZLEM SÜRESİ : **01.10.1996 - 30.09.2006**

ORTALAMA AKIMLAR : **Gözlem süresinde 0.233 m3/sn. (8 Yıllık) 2006 Su yılında 0.159 m3/sn.**

ANLIK EN ÇOK VE EN AZ AKIMLAR:

2006 Su yılında anlık ençok akım	:	**0.325**	**m3/sn**	**25.04.2006**
2006 Su yılında anlık enaz akım	:	**0.038**	**m3/sn**	**11.12.2005**
Gözlem süresinde anlık ençok akım	:	**1.03**	**m3/sn**	**28.04.2000**
Gözlem süresinde anlık enaz akım	:	**0.001**	**m3/sn**	**18.12.1996**

Akımlar 01 Ekim 2005 'den 30 Eylül 2006' a kadar m3/sn olarak

Gün	Ekim	Kasım	Aralık	Ocak	Şubat	Mart	Nisan	Mayıs	Haziran	Temmuz	Ağustos	Eylül
01	0.169	0.135	0.118	0.102	0.088	0.102	0.223	0.305	0.243	0.205	0.152	0.135
02	0.169	0.135	0.118	0.102	0.088	0.102	0.243	0.305	0.243	0.205	0.135	0.135
03	0.169	0.135	0.118	0.102	0.088	0.102	0.243	0.305	0.243	0.205	0.152	0.135
04	0.169	0.135	0.118	0.102	0.088	0.102	0.243	0.284	0.243	0.187	0.152	0.135
05	0.152	0.135	0.118	0.102	0.088	0.102	0.243	0.284	0.243	0.187	0.152	0.135
06	0.152	0.135	0.118	0.102	0.088	0.102	0.243	0.284	0.223	0.187	0.135	0.135
07	0.152	0.135	0.118	0.102	0.088	0.118	0.264	0.264	0.243	0.187	0.135	0.118
08	0.169	0.118	0.118	0.102	0.088	0.118	0.264	0.264	0.223	0.169	0.135	0.118
09	0.169	0.118	0.102	0.102	0.088	0.118	0.284	0.264	0.223	0.187	0.152	0.118
10	0.152	0.118	0.102	0.102	0.088	0.118	0.284	0.264	0.223	0.187	0.152	0.118
11	0.135	0.118	0.118	0.102	0.088	0.118	0.284	0.284	0.223	0.169	0.135	0.118
12	0.135	0.118	0.102	0.102	0.088	0.118	0.264	0.284	0.205	0.169	0.135	0.118
13	0.135	0.118	0.102	0.102	0.102	0.118	0.264	0.284	0.187	0.169	0.135	0.118
14	0.135	0.118	0.102	0.102	0.088	0.135	0.264	0.284	0.205	0.169	0.118	0.118
15	0.135	0.118	0.102	0.102	0.088	0.152	0.264	0.284	0.187	0.169	0.135	0.118
16	0.135	0.118	0.102	0.102	0.088	0.169	0.264	0.284	0.223	0.187	0.118	0.118
17	0.135	0.118	0.102	0.102	0.088	0.187	0.264	0.284	0.205	0.152	0.152	0.118
18	0.135	0.135	0.102	0.102	0.088	0.187	0.264	0.284	0.223	0.169	0.135	0.118
19	0.135	0.135	0.102	0.088	0.088	0.187	0.264	0.284	0.205	0.152	0.135	0.118
20	0.135	0.118	0.102	0.102	0.088	0.187	0.284	0.284	0.205	0.135	0.135	0.118
21	0.135	0.135	0.102	0.088	0.088	0.187	0.284	0.264	0.169	0.169	0.135	0.118
22	0.135	0.118	0.102	0.088	0.088	0.187	0.284	0.264	0.169	0.135	0.152	0.118
23	0.135	0.118	0.102	0.088	0.088	0.187	0.305	0.264	0.152	0.152	0.152	0.118
24	0.135	0.118	0.102	0.088	0.088	0.187	0.305	0.264	0.152	0.152	0.152	0.135
25	0.135	0.118	0.102	0.088	0.088	0.205	0.284	0.264	0.169	0.152	0.152	0.135
26	0.135	0.135	0.102	0.088	0.088	0.205	0.284	0.264	0.169	0.135	0.152	0.135
27	0.135	0.118	0.102	0.088	0.088	0.205	0.305	0.264	0.169	0.135	0.135	0.135
28	0.135	0.118	0.102	0.088	0.088	0.205	0.305	0.264	0.187	0.135	0.135	0.135
29	0.135	0.118	0.102	0.088	-----	0.223	0.305	0.243	0.187	0.135	0.135	0.135
30	0.135	0.118	0.102	0.088	-----	0.223	0.305	0.243	0.205	0.135	0.152	0.135
31	0.135	-----	0.102	0.088	-----	0.223	-----	0.243	-----	0.135	0.135	-----
Maks.	0.284	0.264	0.223	0.118	0.118	0.223	0.325	0.305	0.243	0.205	0.169	0.152
Min.	0.074	0.088	0.038	0.060	0.074	0.088	0.223	0.243	0.135	0.118	0.118	0.118
Ortalama	0.144	0.124	0.107	0.097	0.089	0.157	0.273	0.274	0.205	0.165	0.141	0.125
LT/SN/Km2	7.15	6.18	5.31	4.81	4.40	7.83	13.6	13.6	10.2	8.21	7.02	6.24
AKIM mm.	19.2	16.0	14.2	12.9	10.7	21.0	35.2	36.6	26.4	22.0	18.8	16.2
MİL. M3	0.385	0.322	0.286	0.259	0.214	0.422	0.707	0.735	0.531	0.442	0.378	0.325

SU YILI (2006) YILLIK TOPLAM AKIM 5.01 MİLYON M3 249 MM. 7.9 LT/SN/Km2

15. Kizilirmak Havzasi

D15A276 KARABOĞAZ DERESİ ŞENYURT

YERİ : **SİVAS ULAŞ İLÇESİ ŞENYURT KÖYÜ ÇIKIŞINDADIR**
37°19'55" Doğu - 39°27'9" Kuzey

YAĞIŞ ALANI : **11,90 km2** **YAKLAŞIK KOT : 1643 m**

GÖZLEM SÜRESİ : **01.10.1997 - 30.09.2006**

ORTALAMA AKIMLAR : **Gözlem süresinde 0.079 m3/sn. (9 Yıllık) 2006 Su yılında 0.084 m3/sn.**

ANLIK EN ÇOK VE EN AZ AKIMLAR:

2006 Su yılında anlık ençok akım	**:**	**0.670 m3/sn**	**01.04.2006**
2006 Su yılında anlık enaz akım	**:**	**0.000 m3/sn**	**10.08.2006**
Gözlem süresinde anlık ençok akım	**:**	**5.36 m3/sn**	**05.06.1998**
Gözlem süresinde anlık enaz akım	**:**	**0.000 m3/sn**	**01.08.2000**

Akımlar 01 Ekim 2005 'den 30 Eylül 2006' a kadar m3/sn olarak

Gün	Ekim	Kasım	Aralık	Ocak	Şubat	Mart	Nisan	Mayıs	Haziran	Temmuz	Ağustos	Eylül
01	0.004	0.007	0.012	0.027	0.012	0.012	0.520	0.310	0.120	0.002	0.038	0.002
02	0.004	0.007	0.012	0.027	0.012	0.012	0.620	0.350	0.063	0.018	0.038	0.002
03	0.004	0.007	0.012	0.027	0.012	0.012	0.570	0.310	0.012	0.018	0.038	0.002
04	0.012	0.007	0.012	0.027	0.012	0.018	0.570	0.310	0.018	0.018	0.038	0.007
05	0.018	0.018	0.012	0.027	0.012	0.018	0.470	0.310	0.018	0.018	0.038	0.007
06	0.018	0.018	0.012	0.027	0.012	0.018	0.470	0.310	0.038	0.027	0.038	0.012
07	0.018	0.018	0.012	0.027	0.012	0.018	0.410	0.310	0.050	0.027	0.038	0.004
08	0.018	0.018	0.012	0.027	0.012	0.050	0.410	0.310	0.038	0.038	0.038	0.007
09	0.018	0.018	0.018	0.027	0.012	0.120	0.470	0.310	0.038	0.038	0.038	0.012
10	0.018	0.018	0.018	0.027	0.012	0.098	0.470	0.282	0.063	0.027	KURU	0.004
11	0.018	0.012	0.018	0.027	0.012	0.098	0.410	0.254	0.081	0.038	KURU	0.012
12	0.018	0.007	0.018	0.027	0.018	0.098	0.390	0.254	0.063	0.038	KURU	0.018
13	0.018	0.007	0.018	0.027	0.012	0.144	0.350	0.254	0.063	0.038	KURU	0.018
14	0.018	0.007	0.018	0.027	0.012	0.144	0.310	0.254	0.063	0.038	0.004	0.012
15	0.018	0.007	0.018	0.027	0.012	0.198	0.310	0.254	0.050	0.038	0.007	0.012
16	0.018	0.012	0.018	0.027	0.012	0.198	0.310	0.254	0.063	0.038	0.018	0.012
17	0.027	0.012	0.018	0.027	0.012	0.226	0.282	0.254	0.050	0.012	0.027	0.012
18	0.027	0.012	0.018	0.027	0.007	0.254	0.254	0.254	0.038	0.001	0.027	0.012
19	0.027	0.012	0.018	0.027	0.012	0.254	0.254	0.254	0.012	0.001	0.007	0.007
20	0.027	0.012	0.027	0.098	0.012	0.254	0.254	0.198	0.007	0.001	KURU	0.004
21	0.027	0.012	0.027	0.170	0.012	0.254	0.226	0.198	0.002	0.027	KURU	0.012
22	0.027	0.012	0.027	0.170	0.012	0.254	0.226	0.198	0.050	0.012	0.004	0.012
23	0.027	0.012	0.027	0.170	0.012	0.254	0.226	0.198	0.027	0.004	0.002	0.012
24	0.027	0.012	0.027	0.063	0.012	0.310	0.310	0.198	0.038	0.012	0.004	0.004
25	0.038	0.012	0.027	0.012	0.012	0.410	0.350	0.198	0.038	0.038	0.018	KURU
26	0.038	0.012	0.027	0.012	0.012	0.410	0.282	0.170	0.027	0.038	0.018	KURU
27	0.018	0.012	0.027	0.012	0.012	0.410	0.254	0.170	0.007	0.038	0.012	KURU
28	0.007	0.012	0.027	0.012	0.012	0.410	0.254	0.170	0.002	0.038	0.002	0.004
29	0.007	0.012	0.027	0.012	-----	0.410	0.254	0.170	0.001	0.038	0.002	0.007
30	0.007	0.012	0.027	0.012	-----	0.470	0.350	0.144	0.001	0.038	0.002	0.007
31	0.007	-----	0.027	0.012	-----	0.470	-----	0.120	-----	0.038	0.002	-----
Maks.	0.038	0.018	0.027	0.198	0.050	0.570	0.670	0.390	0.144	0.050	0.038	0.027
Min.	0.004	0.007	0.012	0.004	0.001	0.012	0.198	0.120	0.001	0.001	KURU	KURU
Ortalama	0.019	0.012	0.020	0.041	0.012	0.203	0.361	0.243	0.038	0.026	0.016	0.008
LT/SN/Km2	1.57	0.997	1.68	3.44	1.01	17.1	30.4	20.4	3.20	2.16	1.35	0.661
AKIM mm.	4.20	2.58	4.49	9.21	2.45	45.8	78.7	54.7	8.28	5.77	3.62	1.71
MİL. M3	0.050	0.031	0.053	0.110	0.029	0.545	0.936	0.651	0.099	0.069	0.043	0.020

SU YILI (2006) YILLIK TOPLAM AKIM 2.64 MİLYON M3 222 MM. 7.0 LT/SN/Km2

15. Kizilirmak Havzasi

D15A277 KARANLIK DERE ÖRENLİCE

YERİ : **SİVAS ULAŞ İLÇESİ ÖRENLİCE KÖYÜ İLE ŞENYURT KÖYÜ ARASINDADIR**
37°18'3" Doğu - 39°26'53" Kuzey

YAĞIŞ ALANI : **38,00 km2** **YAKLAŞIK KOT : 1570 m**

GÖZLEM SÜRESİ : **01.10.1997 - 30.09.2006**

ORTALAMA AKIMLAR : **Gözlem süresinde 0.434 m3/sn. (9 Yıllık) 2006 Su yılında 0.334 m3/sn.**

ANLIK EN ÇOK VE EN AZ AKIMLAR:

2006 Su yılında anlık ençok akım	:	**5.37**	**m3/sn**	**30.04.2006**
2006 Su yılında anlık enaz akım	:	**0.098**	**m3/sn**	**21.07.2006**
Gözlem süresinde anlık ençok akım	:	**35.4**	**m3/sn**	**10.06.1998**
Gözlem süresinde anlık enaz akım	:	**0.005**	**m3/sn**	**01.09.2002**

Akımlar 01 Ekim 2005 'den 30 Eylül 2006' a kadar m3/sn olarak

Gün	Ekim	Kasım	Aralık	Ocak	Şubat	Mart	Nisan	Mayıs	Haziran	Temmuz	Ağustos	Eylül
01	0.160	0.135	0.160	0.185	0.185	0.251	1.05	1.05	0.458	0.284	0.117	0.098
02	0.160	0.135	0.160	0.185	0.185	0.284	1.05	1.55	0.458	0.284	0.098	0.098
03	0.160	0.135	0.160	0.185	0.185	0.350	1.15	1.25	0.458	0.284	0.117	0.098
04	0.160	0.135	0.160	0.185	0.185	0.350	1.15	1.15	0.458	0.218	0.117	0.098
05	0.160	0.185	0.160	0.185	0.185	0.404	0.964	1.05	0.458	0.218	0.117	0.098
06	0.160	0.185	0.160	0.185	0.185	0.458	0.964	1.05	0.458	0.218	0.117	0.098
07	0.160	0.185	0.160	0.185	0.185	0.566	0.964	1.05	0.458	0.218	0.117	0.098
08	0.160	0.185	0.160	0.185	0.185	0.706	0.964	1.05	0.458	0.218	0.117	0.098
09	0.160	0.185	0.160	0.185	0.185	0.706	1.05	1.05	0.458	0.218	0.117	0.098
10	0.160	0.185	0.185	0.218	0.185	0.566	1.05	1.05	0.458	0.185	0.117	0.098
11	0.160	0.185	0.185	0.185	0.185	0.566	0.964	1.05	0.458	0.185	0.117	0.098
12	0.135	0.160	0.185	0.185	0.185	0.620	0.878	0.878	0.350	0.218	0.117	0.098
13	0.135	0.160	0.185	0.218	0.185	0.620	0.878	0.878	0.317	0.251	0.117	0.098
14	0.135	0.160	0.185	0.218	0.185	0.620	0.792	0.878	0.317	0.251	0.117	0.098
15	0.135	0.160	0.185	0.185	0.185	0.792	0.792	0.878	0.350	0.251	0.117	0.098
16	0.135	0.160	0.185	0.251	0.284	0.706	0.706	0.878	0.350	0.218	0.117	0.098
17	0.160	0.160	0.185	0.185	0.284	0.620	0.706	0.878	0.317	0.218	0.117	0.098
18	0.160	0.160	0.185	0.185	0.185	0.620	0.620	0.878	0.317	0.218	0.117	0.098
19	0.160	0.160	0.185	0.185	0.185	0.620	0.566	0.878	0.404	0.218	0.098	0.098
20	0.160	0.160	0.185	0.185	0.185	0.566	0.566	0.878	0.317	0.218	0.117	0.098
21	0.160	0.160	0.185	0.251	0.185	0.566	0.512	0.792	0.317	0.160	0.098	0.098
22	0.135	0.160	0.185	0.284	0.185	0.620	0.458	0.792	0.317	0.117	0.117	0.098
23	0.135	0.185	0.185	0.185	0.185	0.620	0.512	0.620	0.317	0.117	0.117	0.098
24	0.160	0.160	0.284	0.185	0.185	0.706	1.05	0.512	0.317	0.117	0.117	0.098
25	0.160	0.160	0.185	0.185	0.185	0.878	1.05	0.512	0.317	0.098	0.098	0.098
26	0.160	0.160	0.185	0.185	0.185	0.878	0.706	0.458	0.317	0.098	0.098	0.098
27	0.135	0.160	0.284	0.185	0.185	0.792	0.620	0.458	0.317	0.098	0.098	0.098
28	0.135	0.160	0.251	0.284	0.218	0.792	0.620	0.458	0.317	0.098	0.117	0.098
29	0.135	0.160	0.185	0.251	-----	0.792	0.792	0.458	0.317	0.098	0.117	0.098
30	0.135	0.160	0.185	0.317	-----	0.792	1.45	0.458	0.317	0.098	0.098	0.098
31	0.135	-----	0.185	0.284	-----	0.964	-----	0.458	-----	0.117	0.098	-----
Maks.	0.160	0.458	0.458	0.458	0.458	1.05	5.37	3.95	0.458	0.284	0.135	0.098
Min.	0.135	0.135	0.135	0.160	0.160	0.251	0.404	0.458	0.284	0.098	0.098	0.098
Ortalama	0.150	0.163	0.186	0.208	0.193	0.626	0.853	0.846	0.375	0.187	0.112	0.098
LT/SN/Km2	3.96	4.30	4.90	5.48	5.09	16.5	22.5	22.3	9.87	4.93	2.95	2.58
AKIM mm.	10.6	11.1	13.1	14.7	12.3	44.1	58.2	59.6	25.6	13.2	7.90	6.68
MİL. M3	0.403	0.423	0.499	0.558	0.468	1.68	2.21	2.27	0.972	0.502	0.300	0.254

SU YILI (2006) YILLIK TOPLAM AKIM 10.54 MİLYON M3 277 MM. 8.8 LT/SN/Km2

15. Kizilirmak Havzasi

D15A278 SOKUÖZÜ DERESİ ÇAĞLAYAN

YERİ : **SİVAS YILDIZELİ İLÇESİ ÇAĞLAYAN KÖYÜ GÜNEYBATISINDAKİ KÜMBET YOLU KÖPRÜSÜNÜN MANSABINDADIR**

36°32'3" Doğu - 39°47'36" Kuzey

YAĞIŞ ALANI : **12,30 km2** **YAKLAŞIK KOT : 1525 m**

GÖZLEM SÜRESİ : **01.10.1997 - 30.09.2006**

ORTALAMA AKIMLAR : **Gözlem süresinde 0.072 m3/sn. (7 Yıllık) 2006 Su yılında 0.043 m3/sn.**

ANLIK EN ÇOK VE EN AZ AKIMLAR:

2006 Su yılında anlık ençok akım	**:**	**1.05**	**m3/sn**	**25.03.2006**
2006 Su yılında anlık enaz akım	**:**	**0.000**	**m3/sn**	**01.10.2005**
Gözlem süresinde anlık ençok akım	**:**	**6.08**	**m3/sn**	**14.07.2002**
Gözlem süresinde anlık enaz akım	**:**	**0.000**	**m3/sn**	**01.10.1997**

Akımlar 01 Ekim 2005 'den 30 Eylül 2006' a kadar m3/sn olarak

Gün	Ekim	Kasım	Aralık	Ocak	Şubat	Mart	Nisan	Mayıs	Haziran	Temmuz	Ağustos	Eylül
01	KURU	KURU	KURU	KURU	KURU	KURU	0.215	0.180	0.092	0.007	KURU	KURU
02	KURU	KURU	KURU	KURU	KURU	KURU	0.265	0.215	0.092	0.007	KURU	KURU
03	KURU	KURU	KURU	KURU	KURU	0.016	0.300	0.180	0.066	0.007	KURU	KURU
04	KURU	KURU	KURU	KURU	KURU	0.029	0.215	0.180	0.066	0.007	KURU	KURU
05	KURU	KURU	KURU	KURU	KURU	0.029	0.215	0.180	0.066	0.007	KURU	KURU
06	KURU	KURU	KURU	KURU	KURU	0.046	0.215	0.180	0.046	0.007	KURU	KURU
07	KURU	KURU	KURU	KURU	KURU	0.066	0.180	0.180	0.046	0.007	KURU	KURU
08	KURU	KURU	KURU	KURU	KURU	0.066	0.180	0.145	0.046	0.007	KURU	KURU
09	KURU	KURU	KURU	KURU	KURU	0.092	0.180	0.145	0.046	0.007	KURU	KURU
10	KURU	KURU	KURU	KURU	KURU	0.092	0.145	0.215	0.046	0.007	KURU	KURU
11	KURU	KURU	KURU	KURU	KURU	0.092	0.145	0.180	0.046	0.007	KURU	KURU
12	KURU	KURU	KURU	KURU	KURU	0.092	0.145	0.145	0.046	0.007	KURU	KURU
13	KURU	KURU	KURU	KURU	KURU	0.092	0.145	0.215	0.046	0.007	KURU	KURU
14	KURU	KURU	KURU	KURU	KURU	0.117	0.117	0.180	0.046	0.004	KURU	KURU
15	KURU	KURU	KURU	KURU	KURU	0.117	0.117	0.145	0.046	0.004	KURU	KURU
16	KURU	KURU	KURU	KURU	KURU	0.117	0.117	0.180	0.029	0.004	KURU	KURU
17	KURU	KURU	KURU	KURU	KURU	0.117	0.117	0.300	0.029	0.004	KURU	KURU
18	KURU	KURU	KURU	KURU	KURU	0.145	0.092	0.265	0.029	0.004	KURU	KURU
19	KURU	KURU	KURU	KURU	KURU	0.145	0.092	0.215	0.029	0.004	KURU	KURU
20	KURU	KURU	KURU	KURU	KURU	0.145	0.066	0.180	0.029	0.004	KURU	KURU
21	KURU	KURU	KURU	KURU	KURU	0.180	0.066	0.180	0.029	0.004	KURU	KURU
22	KURU	KURU	KURU	KURU	KURU	0.265	0.066	0.145	0.029	0.004	KURU	KURU
23	KURU	KURU	KURU	KURU	KURU	0.265	0.092	0.117	0.029	0.004	KURU	KURU
24	KURU	KURU	KURU	KURU	KURU	0.265	0.092	0.117	0.029	0.004	KURU	KURU
25	KURU	KURU	KURU	KURU	KURU	0.614	0.117	0.092	0.016	0.004	KURU	KURU
26	KURU	KURU	KURU	KURU	KURU	0.395	0.117	0.117	0.016	KURU	KURU	KURU
27	KURU	KURU	KURU	KURU	KURU	0.300	0.117	0.180	0.007	KURU	KURU	KURU
28	KURU	KURU	KURU	KURU	KURU	0.265	0.117	0.145	0.007	KURU	KURU	KURU
29	KURU	KURU	KURU	KURU	-----	0.265	0.145	0.117	0.007	KURU	KURU	KURU
30	KURU	KURU	KURU	KURU	-----	0.215	0.215	0.092	0.007	KURU	KURU	KURU
31	KURU	-----	KURU	KURU	-----	0.215	-----	0.092	-----	KURU	KURU	-----
Maks.	KURU	KURU	KURU	KURU	KURU	1.05	0.395	0.556	0.092	0.007	KURU	KURU
Min.	KURU	KURU	KURU	KURU	KURU	KURU	0.066	0.092	0.007	KURU	KURU	KURU
Ortalama	KURU	KURU	KURU	KURU	KURU	0.157	0.147	0.168	0.039	0.004	KURU	KURU
LT/SN/Km2	0.000	0.000	0.000	0.000	0.000	12.7	11.9	13.6	3.15	0.365	0.000	0.000
AKIM mm.	0.000	0.000	0.000	0.000	0.000	34.1	31.0	36.5	8.17	0.976	0.000	0.000
MİL. M3	0.000	0.000	0.000	0.000	0.000	0.420	0.381	0.449	0.100	0.012	0.000	0.000

SU YILI (2006) YILLIK TOPLAM AKIM 1.36 MİLYON M3 111 MM. 3.5 LT/SN/Km2

15. Kizilirmak Havzasi

D15A282 ÇORUHÖZÜ DERESİ BALIŞEYH

YERİ : **ANKARA-ÇORUM YOLU ÜZERİNDEKİ BALIŞEYH İLÇESİNİ 4 KM GEÇİNCE KIRLANGIÇ KÖYÜNE DÖNÜLÜR 300 M İLERİDE KÖPRÜNÜN 50 M MANSABINDADIR. 31°20'34" Doğu - 40°14'25" Kuzey**

YAĞIŞ ALANI : **289.00 km2** **YAKLAŞIK KOT : 870 m**

GÖZLEM SÜRESİ : **15.12.1977 - 30.09.2006**

ORTALAMA AKIMLAR : **Gözlem süresinde 0.197 m3/sn. (4 Yıllık) 2006 Su yılında 0.188 m3/sn.**

ANLIK EN ÇOK VE EN AZ AKIMLAR:

2006 Su yılında anlık ençok akım	**:**	**0.990 m3/sn**	**03.03.2006**
2006 Su yılında anlık enaz akım	**:**	**0.008 m3/sn**	**12.08.2006**
Gözlem süresinde anlık ençok akım	**:**	**7.78 m3/sn**	**31.05.2005**
Gözlem süresinde anlık enaz akım	**:**	**0.008 m3/sn**	**12.08.2006**

İstasyon için kullanılmış anahtar bulunamadı.

Akımlar 01 Ekim 2005 'den 30 Eylül 2006' a kadar m3/sn olarak

Gün	Ekim	Kasım	Aralık	Ocak	Şubat	Mart	Nisan	Mayıs	Haziran	Temmuz	Ağustos	Eylül
01	0.095	0.095	0.095	0.185	0.185	0.640	0.424	0.370	0.185	0.046	0.025	0.011
02	0.095	0.140	0.095	0.140	0.185	0.640	0.478	0.478	0.230	0.065	0.033	0.015
03	0.095	0.140	0.095	0.140	0.185	0.850	0.478	0.478	0.185	0.065	0.033	0.015
04	0.095	0.140	0.095	0.140	0.185	0.920	0.478	0.424	0.230	0.065	0.033	0.015
05	0.095	0.140	0.140	0.140	0.185	0.710	0.478	0.424	0.230	0.065	0.033	0.015
06	0.095	0.140	0.095	0.185	0.185	0.640	0.424	0.478	0.185	0.046	0.025	0.015
07	0.095	0.140	0.140	0.185	0.230	0.586	0.478	0.478	0.185	0.033	0.025	0.011
08	0.095	0.140	0.140	0.185	0.230	0.478	0.478	0.478	0.185	0.033	0.019	0.011
09	0.095	0.095	0.140	0.185	0.230	0.478	0.478	0.478	0.230	0.033	0.015	0.011
10	0.095	0.095	0.140	0.185	0.230	0.424	0.478	0.424	0.230	0.025	0.015	0.011
11	0.095	0.095	0.140	0.185	0.230	0.370	0.275	0.478	0.230	0.025	0.011	0.011
12	0.095	0.095	0.140	0.185	0.320	0.370	0.275	0.424	0.230	0.025	0.011	0.011
13	0.095	0.095	0.140	0.185	0.275	0.370	0.275	0.424	0.230	0.019	0.008	0.011
14	0.095	0.095	0.140	0.185	0.275	0.320	0.275	0.424	0.230	0.019	0.008	0.011
15	0.095	0.095	0.140	0.185	0.275	0.320	0.275	0.424	0.185	0.025	0.011	0.011
16	0.095	0.095	0.140	0.185	0.230	0.320	0.320	0.424	0.230	0.025	0.015	0.015
17	0.140	0.095	0.140	0.185	0.230	0.320	0.275	0.424	0.230	0.046	0.015	0.015
18	0.095	0.095	0.140	0.185	0.230	0.370	0.275	0.424	0.230	0.033	0.015	0.015
19	0.095	0.095	0.140	0.185	0.275	0.478	0.275	0.370	0.230	0.025	0.015	0.015
20	0.140	0.095	0.140	0.185	0.275	0.532	0.275	0.320	0.185	0.025	0.011	0.019
21	0.140	0.140	0.140	0.185	0.275	0.478	0.275	0.320	0.140	0.025	0.008	0.019
22	0.140	0.140	0.140	0.185	0.275	0.424	0.275	0.275	0.140	0.025	0.008	0.230
23	0.140	0.095	0.140	0.185	0.320	0.370	0.320	0.275	0.095	0.025	0.008	0.095
24	0.140	0.095	0.140	0.185	0.320	0.370	0.275	0.275	0.095	0.025	0.008	0.046
25	0.095	0.140	0.140	0.185	0.320	0.478	0.275	0.230	0.046	0.025	0.008	0.046
26	0.095	0.140	0.140	0.185	0.478	0.710	0.275	0.230	0.025	0.025	0.008	0.046
27	0.095	0.140	0.140	0.185	0.710	0.532	0.275	0.275	0.025	0.019	0.008	0.065
28	0.095	0.095	0.140	0.185	0.640	0.478	0.275	0.230	0.019	0.019	0.011	0.065
29	0.095	0.095	0.140	0.185	-----	0.478	0.275	0.185	0.025	0.025	0.011	0.065
30	0.095	0.095	0.140	0.185	-----	0.478	0.320	0.185	0.046	0.025	0.011	0.065
31	0.095	-----	0.140	0.185	-----	0.424	-----	0.185	-----	0.025	0.011	-----
Maks.	0.140	0.230	0.140	0.230	0.920	0.990	0.478	0.532	0.532	0.140	0.046	0.320
Min.	0.046	0.095	0.095	0.140	0.140	0.320	0.275	0.140	0.019	0.015	0.008	0.011
Ortalama	0.104	0.113	0.133	0.179	0.285	0.495	0.344	0.365	0.165	0.032	0.015	0.034
LT/SN/Km2	0.359	0.391	0.459	0.620	0.987	1.71	1.19	1.26	0.570	0.112	0.053	0.116
AKIM mm.	0.961	1.01	1.23	1.66	2.39	4.59	3.08	3.38	1.48	0.301	0.142	0.301
MİL. M3	0.278	0.293	0.356	0.480	0.690	1.33	0.891	0.977	0.427	0.087	0.041	0.087

SU YILI (2006) YILLIK TOPLAM AKIM 5.94 MİLYON M3 21 MM. 0.7 LT/SN/Km2

15. Kizilirmak Havzasi

D15A283 İSLİM DERE HACIALİ

YERİ : **SİVAS MERKEZ HACIALİ KÖYÜNDEDİR**
37°20'55" Doğu - 39°38'50" Kuzey

YAĞIŞ ALANI : **32,10 km2** **YAKLAŞIK KOT : 1455 m**

GÖZLEM SÜRESİ : **01.10.1998 - 30.09.2006**

ORTALAMA AKIMLAR : **Gözlem süresinde 0.097 m3/sn. (7 Yıllık) 2006 Su yılında 0.143 m3/sn.**

ANLIK EN ÇOK VE EN AZ AKIMLAR:

2006 Su yılında anlık ençok akım	**:**	**11.8**	**m3/sn**	**29.04.2006**
2006 Su yılında anlık enaz akım	**:**	**0.006**	**m3/sn**	**01.10.2005**
Gözlem süresinde anlık ençok akım	**:**	**11.8**	**m3/sn**	**29.04.2006**
Gözlem süresinde anlık enaz akım	**:**	**0.000**	**m3/sn**	**24.12.2001**

Akımlar 01 Ekim 2005 'den 30 Eylül 2006' a kadar m3/sn olarak

Gün	Ekim	Kasım	Aralık	Ocak	Şubat	Mart	Nisan	Mayıs	Haziran	Temmuz	Ağustos	Eylül
01	0.006	0.024	0.006	0.024	0.024	0.340	0.340	0.950	0.140	0.105	0.024	0.024
02	0.006	0.024	0.006	0.024	0.006	0.400	0.470	1.47	0.140	0.105	0.024	0.024
03	0.024	0.024	0.006	0.024	0.006	0.470	0.540	1.15	0.140	0.105	0.024	0.024
04	0.024	0.024	0.006	0.024	0.006	0.540	0.470	0.860	0.140	0.105	0.024	0.024
05	0.006	0.105	0.006	0.024	0.006	0.400	0.400	0.770	0.140	0.072	0.024	0.024
06	0.006	0.046	0.006	0.046	0.006	0.400	0.340	0.610	0.140	0.072	0.024	0.024
07	0.006	0.046	0.006	0.046	0.006	0.400	0.340	0.540	0.140	0.072	0.024	0.024
08	0.006	0.046	0.006	0.046	0.006	0.610	0.340	0.470	0.140	0.072	0.024	0.024
09	0.006	0.024	0.006	0.046	0.006	0.610	0.340	0.400	0.140	0.072	0.024	0.024
10	0.006	0.006	0.006	0.046	0.024	0.540	0.340	0.340	0.140	0.072	0.024	0.024
11	0.006	0.006	0.006	0.046	0.046	0.540	0.340	0.230	0.140	0.072	0.024	0.024
12	0.006	0.006	0.006	0.046	0.072	0.470	0.230	0.230	0.140	0.046	0.024	0.024
13	0.006	0.006	0.006	0.046	0.140	0.470	0.230	0.230	0.140	0.046	0.024	0.024
14	0.006	0.006	0.006	0.046	0.140	0.610	0.230	0.230	0.140	0.046	0.024	0.024
15	0.006	0.006	0.006	0.046	0.140	0.540	0.230	0.185	0.140	0.046	0.024	0.024
16	0.006	0.006	0.006	0.046	0.105	0.470	0.185	0.340	0.105	0.046	0.024	0.024
17	0.006	0.006	0.006	0.046	0.105	0.470	0.185	0.470	0.105	0.046	0.024	0.024
18	0.024	0.006	0.006	0.046	0.105	0.470	0.185	0.340	0.105	0.046	0.024	0.024
19	0.072	0.006	0.006	0.024	0.046	0.470	0.140	0.230	0.105	0.046	0.024	0.024
20	0.024	0.006	0.006	0.024	0.046	0.470	0.140	0.230	0.105	0.046	0.024	0.024
21	0.024	0.006	0.006	0.024	0.046	0.470	0.140	0.185	0.105	0.046	0.024	0.024
22	0.024	0.006	0.006	0.024	0.046	0.470	0.140	0.185	0.105	0.046	0.024	0.024
23	0.024	0.006	0.006	0.024	0.046	0.470	0.540	0.185	0.105	0.046	0.024	0.024
24	0.024	0.006	0.006	0.024	0.046	0.400	1.15	0.185	0.105	0.046	0.024	0.024
25	0.024	0.006	0.006	0.024	0.072	0.285	1.70	0.185	0.105	0.046	0.024	0.024
26	0.024	0.006	0.006	0.024	0.185	0.285	0.770	0.185	0.105	0.046	0.024	0.024
27	0.024	0.006	0.006	0.024	0.470	0.340	0.610	0.185	0.105	0.046	0.024	0.024
28	0.024	0.006	0.006	0.024	0.470	0.400	0.470	0.185	0.105	0.046	0.024	0.024
29	0.024	0.006	0.006	0.024	-----	0.340	0.770	0.185	0.105	0.046	0.024	0.024
30	0.024	0.006	0.006	0.024	-----	0.340	1.94	0.185	0.105	0.046	0.024	0.024
31	0.024	-----	0.006	0.024	-----	0.340	-----	0.185	-----	0.046	0.024	-----
Maks.	0.340	0.285	0.006	0.046	0.610	1.25	11.8	7.02	0.140	0.105	0.024	0.024
Min.	0.006	0.006	0.006	0.024	0.006	0.285	0.140	0.072	0.105	0.046	0.024	0.024
Ortalama	0.017	0.016	0.006	0.033	0.087	0.446	0.475	0.397	0.123	0.059	0.024	0.024
LT/SN/Km2	0.525	0.508	0.187	1.04	2.69	13.9	14.8	12.4	3.82	1.85	0.748	0.748
AKIM mm.	1.41	1.32	0.501	2.77	6.52	37.2	38.3	33.1	9.89	4.96	2.00	1.94
MİL. M3	0.045	0.042	0.016	0.089	0.209	1.19	1.23	1.06	0.318	0.159	0.064	0.062

SU YILI (2006) YILLIK TOPLAM AKIM 4.48 MİLYON M3 140 MM. 4.4 LT/SN/Km2

15. Kizilirmak Havzasi

D15A284 KANAKÖZÜ DERESİ CEMEL

YERİ : **SİVAS ŞARKIŞLA İLÇESİ CEMEL BELDESİNDEDİR**
36°29'54" Doğu - 39°16'26" Kuzey

YAĞIŞ ALANI : **172,50 km2** **YAKLAŞIK KOT : 1322 m**

GÖZLEM SÜRESİ : **01.04.1992 - 30.09.2006**

ORTALAMA AKIMLAR : **Gözlem süresinde 0.352 m3/sn. (7 Yıllık) 2006 Su yılında 0.235 m3/sn.**

ANLIK EN ÇOK VE EN AZ AKIMLAR:

2006 Su yılında anlık ençok akım	**:**	**49.3**	**m3/sn**	**28.06.2006**
2006 Su yılında anlık enaz akım	**:**	**0.000**	**m3/sn**	**01.10.2005**
Gözlem süresinde anlık ençok akım	**:**	**61.2**	**m3/sn**	**06.09.2002**
Gözlem süresinde anlık enaz akım	**:**	**0.000**	**m3/sn**	**01.10.1999**

Akımlar 01 Ekim 2005 'den 30 Eylül 2006' a kadar m3/sn olarak

Gün	Ekim	Kasım	Aralık	Ocak	Şubat	Mart	Nisan	Mayıs	Haziran	Temmuz	Ağustos	Eylül
01	KURU	0.015	0.029	0.052	0.021	0.450	0.738	1.17	0.390	0.270	0.039	KURU
02	KURU	0.015	0.029	0.052	0.021	0.634	0.738	1.83	0.320	0.210	0.039	KURU
03	0.072	0.015	0.029	0.052	0.029	0.738	0.946	1.65	0.270	0.210	0.039	KURU
04	0.052	0.015	0.029	0.052	0.039	0.842	0.946	1.53	0.210	0.165	0.039	KURU
05	0.039	0.021	0.029	0.052	0.039	0.738	0.842	1.41	0.210	0.135	0.029	KURU
06	0.029	0.015	0.029	0.052	0.052	0.634	0.842	1.29	0.165	0.135	0.029	KURU
07	0.029	0.015	0.029	0.052	0.052	0.634	0.842	1.17	0.135	0.135	0.029	KURU
08	0.029	0.015	0.039	0.072	0.072	0.738	0.738	1.17	0.135	0.135	0.029	KURU
09	0.021	0.015	0.039	0.072	0.105	0.634	0.738	1.17	0.135	0.105	0.029	KURU
10	0.021	0.015	0.039	0.072	0.105	0.634	0.738	1.05	0.135	0.072	KURU	KURU
11	0.021	0.015	0.039	0.072	0.135	0.530	0.634	0.946	0.135	0.052	KURU	KURU
12	0.029	0.015	0.039	0.072	0.165	0.530	0.634	0.842	0.165	0.052	KURU	KURU
13	0.021	0.015	0.039	0.072	0.270	0.530	0.530	0.842	0.135	0.052	KURU	KURU
14	0.021	0.015	0.039	0.072	0.270	0.450	0.530	0.842	0.072	0.052	KURU	KURU
15	0.021	0.015	0.039	0.052	0.270	0.320	0.450	0.842	0.072	0.052	KURU	KURU
16	0.021	0.015	0.052	0.072	0.210	0.390	0.450	0.842	0.072	0.052	KURU	KURU
17	0.021	0.015	0.052	0.052	0.210	0.450	0.450	0.738	0.072	0.052	KURU	KURU
18	0.029	0.015	0.052	0.052	0.320	0.450	0.450	0.738	0.105	0.039	KURU	KURU
19	0.029	0.021	0.052	0.052	0.320	0.450	0.390	0.738	0.105	0.039	KURU	KURU
20	0.021	0.021	0.052	0.052	0.320	0.450	0.390	0.738	0.105	0.039	KURU	KURU
21	0.021	0.021	0.052	0.052	0.270	0.390	0.390	0.842	0.105	0.039	KURU	KURU
22	0.021	0.021	0.052	0.052	0.270	0.450	0.210	0.842	0.072	0.039	KURU	KURU
23	0.015	0.015	0.072	0.052	0.270	0.450	0.320	0.842	0.072	0.039	KURU	KURU
24	0.015	0.015	0.052	0.072	0.270	0.450	0.738	0.738	0.072	0.039	KURU	KURU
25	0.015	0.021	0.052	0.052	0.270	0.738	0.946	0.634	0.072	0.039	KURU	KURU
26	0.021	0.021	0.052	0.052	0.320	1.17	0.842	0.530	0.052	0.039	KURU	KURU
27	0.021	0.021	0.052	0.052	0.390	0.946	0.842	0.634	0.052	0.039	KURU	KURU
28	0.021	0.021	0.052	0.052	0.390	0.842	0.738	0.634	0.738	0.039	KURU	KURU
29	0.021	0.021	0.052	0.039	-----	0.842	0.634	0.530	0.842	0.039	KURU	KURU
30	0.015	0.029	0.052	0.029	-----	0.738	1.17	0.450	0.390	0.039	KURU	KURU
31	0.015	-----	0.052	0.021	-----	0.738	-----	0.390	-----	0.039	KURU	-----
Maks.	5.48	0.039	0.105	0.135	0.450	1.41	1.29	4.18	49.3	0.320	0.039	KURU
Min.	KURU	0.008	0.029	0.021	0.015	0.135	0.135	0.390	0.052	0.011	KURU	KURU
Ortalama	0.023	0.017	0.044	0.056	0.196	0.612	0.662	0.923	0.187	0.080	0.010	KURU
LT/SN/Km2	0.136	0.101	0.256	0.323	1.13	3.55	3.83	5.35	1.08	0.464	0.056	0.000
AKIM mm.	0.364	0.262	0.685	0.864	2.74	9.51	9.94	14.3	2.81	1.24	0.151	0.000
MİL. M3	0.063	0.045	0.118	0.149	0.473	1.64	1.71	2.47	0.485	0.214	0.026	0.000

SU YILI (2006) YILLIK TOPLAM AKIM 7.39 MİLYON M3 43 MM. 1.4 LT/SN/Km2

15. Kizilırmak Havzasi

D15A285 BAKIR Ç. MERYEMDERE

YERİ : HAVZA-VEZİRKÖPRÜ YOLU KÖPRÜBAŞI MEVKİİNDEN SOLA AYRILAN KÖY YOLUNUN 2 KM AŞAĞI MERYEMDERE MAHALLESİNDEDİR. 25 LİK PAFTADAKİ YERİ: F35-D4
35°30'24" Doğu - 41°1'55" Kuzey

YAĞIŞ ALANI : 42,00 km2 YAKLAŞIK KOT : 685 m

GÖZLEM SÜRESİ : 17.12.1998 - 30.09.2006

ORTALAMA AKIMLAR : Gözlem süresinde 0.327 m3/sn. (6 Yıllık) 2006 Su yılında 0.295 m3/sn.

ANLIK EN ÇOK VE EN AZ AKIMLAR:

2006 Su yılında anlık ençok akım	:	8.20	m3/sn	31.07.2006
2006 Su yılında anlık enaz akım	:	0.000	m3/sn	12.08.2006
Gözlem süresinde anlık ençok akım	:	59.2	m3/sn	09.06.1999
Gözlem süresinde anlık enaz akım	:	0.000	m3/sn	12.08.2006

3. Anahtar Eğrisi (Seviyeler cm olarak)

Seviye	Akım	Seviye	Akım	Seviye	Akım	Seviye	Akım
3	0.000	15	0.074	46	3.0	140	64.0
5	0.000	18	0.150	60	6.4	160	88.0
7	0.003	22	0.320	80	14.5	170	100.
10	0.013	29	0.800	100	27.0	190	130.
12	0.028	35	1.4	120	42.2	200	144.

Akımlar 01 Ekim 2005 'den 30 Eylül 2006' a kadar m3/sn olarak

Gün	Ekim	Kasım	Aralık	Ocak	Şubat	Mart	Nisan	Mayıs	Haziran	Temmuz	Ağustos	Eylül
01	0.010	0.013	0.120	0.097	0.019	1.52	1.09	0.275	0.380	0.039	0.440	0.019
02	0.008	0.019	0.097	0.074	0.019	1.30	1.09	0.275	0.275	0.028	0.275	0.028
03	0.013	0.057	0.074	0.074	0.013	1.64	1.20	0.320	0.230	0.019	0.190	0.028
04	0.008	0.380	0.074	0.074	0.013	1.52	1.20	0.275	0.190	0.019	0.074	0.019
05	0.008	0.575	0.057	0.120	0.013	1.09	1.20	0.275	0.190	0.019	0.074	0.019
06	0.008	0.275	0.074	0.275	0.019	1.09	1.20	0.275	0.190	0.019	0.039	0.019
07	0.008	0.120	0.074	0.440	0.097	1.30	1.20	0.275	0.190	0.019	0.039	0.019
08	0.008	0.097	0.074	0.320	0.097	1.64	1.20	0.190	0.120	0.057	0.019	0.019
09	0.008	0.097	0.074	0.230	0.074	1.52	1.20	0.190	0.120	0.057	0.010	0.019
10	0.008	0.039	0.074	0.230	0.097	0.992	1.20	0.190	0.190	0.039	0.005	0.019
11	0.008	0.039	0.074	0.190	0.440	0.650	1.20	0.190	0.190	0.039	0.001	0.019
12	0.008	0.039	0.074	0.190	0.440	0.575	1.20	0.190	0.190	0.028	0.001	0.019
13	0.008	0.028	0.057	0.190	0.230	0.650	1.09	0.190	0.150	0.019	0.002	0.019
14	0.008	0.028	0.039	0.097	0.190	0.992	0.992	0.190	0.150	0.019	0.002	0.019
15	0.008	0.028	0.028	0.057	0.150	1.09	0.800	0.150	0.150	0.019	0.002	0.019
16	0.008	0.019	0.028	0.028	0.150	0.890	0.725	0.150	0.150	0.019	0.002	0.019
17	0.019	0.028	0.039	0.039	0.440	0.800	0.650	0.230	0.150	0.019	0.002	0.019
18	0.010	0.028	0.028	0.057	0.190	0.650	0.575	0.500	0.150	0.019	0.002	0.019
19	0.008	0.039	0.028	0.028	0.097	0.650	0.500	0.575	0.150	0.019	0.002	0.013
20	0.008	0.039	0.028	0.039	0.190	0.575	0.500	0.500	0.120	0.019	0.002	0.013
21	0.008	0.120	0.028	0.039	0.230	0.650	0.440	0.500	0.120	0.019	0.001	0.013
22	0.008	0.320	0.028	0.028	0.275	0.800	0.440	0.380	0.097	0.019	0.001	0.097
23	0.008	0.190	0.019	0.019	0.440	1.30	0.440	0.320	0.074	0.019	0.001	0.039
24	0.008	0.120	0.019	0.019	0.500	1.76	0.440	0.275	0.074	0.039	0.001	0.028
25	0.013	0.120	0.019	0.019	0.890	1.64	0.440	0.190	0.074	0.028	0.001	0.028
26	0.013	0.500	0.028	0.019	1.30	1.09	0.440	0.190	0.057	0.028	0.001	0.074
27	0.013	0.650	0.028	0.019	1.30	0.992	0.380	1.09	0.057	0.074	0.001	0.028
28	0.013	0.500	0.028	0.019	0.992	1.09	0.380	1.09	0.057	0.500	0.001	0.013
29	0.013	0.320	0.028	0.019	-----	1.09	0.320	0.725	0.057	5.65	0.039	0.013
30	0.013	0.190	0.028	0.019	-----	1.09	0.320	0.575	0.057	5.40	0.028	0.013
31	0.013	-----	0.057	0.019	-----	1.09	-----	0.440	-----	1.30	0.028	-----
Maks.	0.028	2.17	0.190	0.440	1.52	2.50	1.52	1.52	0.440	8.20	0.500	0.380
Min.	0.008	0.010	0.019	0.019	0.010	0.575	0.275	0.150	0.057	0.013	KURU	0.013
Ortalama	0.010	0.167	0.049	0.100	0.318	1.09	0.802	0.361	0.145	0.439	0.041	0.024
LT/SN/Km2	0.233	3.98	1.17	2.37	7.57	25.9	19.1	8.59	3.45	10.5	0.988	0.581
AKIM mm.	0.623	10.3	3.14	6.35	18.3	69.4	49.5	23.0	8.95	28.0	2.65	1.51
MİL. M3	0.026	0.433	0.132	0.267	0.769	2.91	2.08	0.966	0.376	1.18	0.111	0.063

SU YILI (2006) YILLIK TOPLAM AKIM 9.31 MİLYON M3 222 MM. 7.0 LT/SN/Km2

15. Kizilirmak Havzasi

D15A286 BUDAKÖZÜ DERESİ KIRANKIŞLA

YERİ : **ÇORUM-SUNGURLU KARAYOLUNUN 60 KM.'SİNDEN 3 KM. MESAFEDE KIRANKIŞLA KÖYÜNÜN GÜNEYİNDE BUDAKÖZÜ DERESİ ÜZERİNDE YER ALMAKTADIR.**
32°5'58" Doğu - 40°17'43" Kuzey

YAĞIŞ ALANI : **435.00 km2** **YAKLAŞIK KOT : 820 m**

GÖZLEM SÜRESİ : **15.12.1998 - 30.09.2006**

ORTALAMA AKIMLAR : **Gözlem süresinde 0.594 m3/sn. (3 Yıllık) 2006 Su yılında 0.999 m3/sn.**

ANLIK EN ÇOK VE EN AZ AKIMLAR:

2006 Su yılında anlık ençok akım	**:**	**21.6**	**m3/sn**	**29.06.2006**
2006 Su yılında anlık enaz akım	**:**	**0.002**	**m3/sn**	**07.06.2006**
Gözlem süresinde anlık ençok akım	**:**	**21.6**	**m3/sn**	**29.06.2006**
Gözlem süresinde anlık enaz akım	**:**	**0.000**	**m3/sn**	**06.06.2003**

İstasyon için kullanılmış anahtar bulunamadı.

Akımlar 01 Ekim 2005 'den 30 Eylül 2006' a kadar m3/sn olarak

Gün	Ekim	Kasım	Aralık	Ocak	Şubat	Mart	Nisan	Mayıs	Haziran	Temmuz	Ağustos	Eylül
01	0.059	0.138	1.33	0.330	0.260	7.92	3.27	0.920	0.033	0.700	0.009	0.009
02	0.059	0.138	1.33	0.330	0.260	6.99	3.27	1.18	0.033	0.700	0.009	0.059
03	0.059	0.190	1.18	0.330	0.260	9.10	3.27	1.18	0.009	0.700	0.009	0.033
04	0.059	0.190	1.18	0.260	0.260	7.22	2.85	1.05	0.004	0.590	0.009	0.033
05	0.059	0.260	1.18	0.260	0.260	5.15	2.49	1.05	0.004	0.330	0.009	0.033
06	0.059	0.260	0.920	0.260	0.260	4.65	2.49	0.920	0.004	0.190	0.009	0.033
07	0.059	0.260	0.700	0.260	0.260	4.90	2.49	0.920	0.004	0.138	0.009	0.033
08	0.059	0.260	0.700	0.260	0.260	5.38	2.31	0.920	0.004	0.138	0.009	0.033
09	0.059	0.260	0.590	0.330	0.330	5.38	2.13	0.810	0.002	0.138	0.009	0.033
10	0.059	0.260	0.260	0.330	0.330	3.69	2.31	0.810	0.009	0.095	0.009	0.033
11	0.059	0.260	0.190	0.330	2.31	3.06	2.31	0.700	0.033	0.095	0.009	0.033
12	0.059	0.260	0.190	0.330	5.15	2.67	2.13	0.700	0.033	0.095	0.009	0.033
13	0.059	0.260	0.190	0.330	3.27	2.85	1.95	0.700	0.033	0.095	0.009	0.033
14	0.059	0.260	0.190	0.330	2.49	4.65	1.80	0.700	0.059	0.095	0.009	0.033
15	0.059	0.330	0.190	0.330	1.95	6.53	2.13	0.700	0.059	0.095	0.009	0.033
16	0.059	0.410	0.190	0.330	1.64	4.40	2.13	0.700	0.095	0.095	0.009	0.033
17	0.095	0.410	0.190	0.330	1.80	4.40	1.80	0.700	0.095	0.095	0.009	0.033
18	0.095	0.410	0.190	0.330	1.33	3.69	1.64	0.590	0.059	0.095	0.009	0.033
19	0.095	0.410	0.190	0.330	1.95	5.15	1.49	0.700	0.059	0.095	0.009	0.033
20	0.095	0.920	0.190	0.330	2.31	7.22	1.49	0.700	0.059	0.095	0.009	0.018
21	0.095	3.06	0.190	0.330	2.31	9.10	1.33	0.700	0.059	0.059	0.009	0.059
22	0.095	1.64	0.190	0.330	2.49	9.80	1.33	0.590	0.059	0.059	0.009	0.095
23	0.095	1.49	0.190	0.260	2.67	8.16	1.33	0.410	0.059	0.059	0.009	0.095
24	0.095	1.33	0.190	0.260	3.06	6.53	1.18	0.330	0.059	0.059	0.009	0.059
25	0.095	1.33	0.190	0.260	4.15	6.76	1.18	0.138	0.059	0.059	0.009	0.095
26	0.095	1.33	0.190	0.260	5.61	6.30	1.18	0.138	0.059	0.018	0.009	0.095
27	0.095	1.33	0.190	0.260	6.53	5.15	1.05	0.059	0.059	0.018	0.009	0.095
28	0.095	1.33	0.260	0.260	5.61	4.40	1.05	0.033	0.059	0.018	0.009	0.095
29	0.095	1.33	0.260	0.260	-----	3.90	0.920	0.033	0.810	0.018	0.009	0.059
30	0.095	1.33	0.330	0.260	-----	3.69	0.920	0.033	0.920	0.018	0.009	0.059
31	0.095	-----	0.330	0.260	-----	3.48	-----	0.033	-----	0.009	0.009	-----
Maks.	0.138	6.99	1.49	0.410	8.63	16.3	3.69	1.80	21.6	0.700	0.009	0.920
Min.	0.059	0.095	0.138	0.190	0.260	2.49	0.920	0.033	0.002	0.004	0.009	0.004
Ortalama	0.076	0.722	0.445	0.298	2.12	5.56	1.91	0.618	0.096	0.163	0.009	0.048
LT/SN/Km2	0.176	1.66	1.02	0.686	4.87	12.8	4.38	1.42	0.222	0.375	0.021	0.111
AKIM mm.	0.471	4.30	2.74	1.84	11.8	34.2	11.4	3.80	0.574	1.01	0.055	0.289
MİL. M3	0.205	1.87	1.19	0.799	5.13	14.9	4.94	1.65	0.250	0.437	0.024	0.126

SU YILI (2006) YILLIK TOPLAM AKIM 31.52 MİLYON M3 72 MM. 2.3 LT/SN/Km2

15. Kizilirmak Havzasi

D15A288 ARİFEGAZİLİ DERESİ ARİFEGAZİLİ

YERİ : **ÇORUM-SUNGURLU KARAYOLUNUN 60 KM.SİNDE YOLUN GÜNEYİNDE VE ANAYOLA 200 M. UZAKLIKTADIR**

34°40'41" Doğu - 40°11'48" Kuzey

YAĞIŞ ALANI : **153.00 km2** **YAKLAŞIK KOT : 850 m**

GÖZLEM SÜRESİ : **15.12.1998 - 30.09.2006**

ORTALAMA AKIMLAR : **Gözlem süresinde 0.085 m3/sn. (4 Yıllık) 2006 Su yılında 0.115 m3/sn.**

ANLIK EN ÇOK VE EN AZ AKIMLAR:

2006 Su yılında anlık ençok akım	**:**	**1.18**	**m3/sn**	**20.03.2006**
2006 Su yılında anlık enaz akım	**:**	**0.003**	**m3/sn**	**01.06.2006**
Gözlem süresinde anlık ençok akım	**:**	**2.71**	**m3/sn**	**03.03.2005**
Gözlem süresinde anlık enaz akım	**:**	**0.000**	**m3/sn**	**25.07.2004**

İstasyon için kullanılmış anahtar bulunamadı.

Akımlar 01 Ekim 2005 'den 30 Eylül 2006' a kadar m3/sn olarak

Gün	Ekim	Kasım	Aralık	Ocak	Şubat	Mart	Nisan	Mayıs	Haziran	Temmuz	Ağustos	Eylül
01	0.036	0.080	0.080	0.080	0.109	0.831	0.426	0.145	0.010	0.036	0.021	0.036
02	0.036	0.080	0.080	0.080	0.109	0.599	0.508	0.145	0.003	0.036	0.021	0.080
03	0.036	0.080	0.080	0.080	0.109	0.831	0.508	0.145	0.003	0.036	0.021	0.055
04	0.036	0.080	0.055	0.080	0.109	0.508	0.426	0.145	0.003	0.036	0.021	0.036
05	0.036	0.080	0.055	0.080	0.109	0.358	0.426	0.187	0.003	0.036	0.021	0.036
06	0.036	0.080	0.055	0.080	0.109	0.358	0.358	0.237	0.003	0.036	0.021	0.036
07	0.036	0.080	0.055	0.080	0.109	0.290	0.358	0.290	0.003	0.036	0.021	0.036
08	0.036	0.080	0.055	0.080	0.145	0.290	0.358	0.290	0.003	0.036	0.021	0.036
09	0.036	0.080	0.055	0.080	0.145	0.358	0.358	0.237	0.003	0.036	0.021	0.036
10	0.036	0.080	0.055	0.080	0.145	0.290	0.358	0.145	0.003	0.036	0.021	0.036
11	0.036	0.080	0.055	0.080	0.145	0.290	0.358	0.145	0.003	0.036	0.021	0.036
12	0.036	0.080	0.055	0.080	0.145	0.290	0.358	0.109	0.003	0.036	0.021	0.036
13	0.036	0.080	0.055	0.080	0.109	0.290	0.290	0.109	0.003	0.036	0.021	0.036
14	0.036	0.080	0.055	0.080	0.145	0.290	0.237	0.055	0.003	0.036	0.021	0.036
15	0.036	0.080	0.055	0.080	0.145	0.290	0.237	0.055	0.003	0.036	0.021	0.036
16	0.036	0.080	0.055	0.080	0.109	0.290	0.290	0.036	0.003	0.036	0.021	0.036
17	0.036	0.080	0.055	0.055	0.109	0.290	0.290	0.036	0.003	0.036	0.021	0.036
18	0.036	0.080	0.055	0.055	0.109	0.290	0.290	0.036	0.003	0.036	0.021	0.036
19	0.036	0.080	0.055	0.055	0.109	0.426	0.290	0.036	0.003	0.036	0.021	0.036
20	0.036	0.109	0.055	0.055	0.109	0.599	0.290	0.021	0.003	0.036	0.021	0.036
21	0.036	0.358	0.055	0.055	0.109	0.715	0.290	0.021	0.003	0.036	0.021	0.036
22	0.036	0.237	0.055	0.080	0.109	0.599	0.290	0.021	0.003	0.036	0.021	0.036
23	0.055	0.109	0.055	0.080	0.109	0.508	0.290	0.021	0.003	0.021	0.021	0.080
24	0.055	0.080	0.055	0.080	0.109	0.508	0.290	0.021	0.003	0.010	0.021	0.055
25	0.055	0.080	0.055	0.080	0.109	0.599	0.290	0.021	0.003	0.021	0.021	0.055
26	0.055	0.080	0.055	0.080	0.145	0.715	0.237	0.010	0.003	0.021	0.021	0.055
27	0.055	0.080	0.055	0.109	0.237	0.599	0.237	0.010	0.003	0.021	0.021	0.055
28	0.080	0.080	0.080	0.109	0.358	0.508	0.187	0.010	0.003	0.021	0.021	0.055
29	0.080	0.055	0.080	0.109	-----	0.508	0.187	0.010	0.021	0.021	0.021	0.055
30	0.080	0.055	0.080	0.109	-----	0.508	0.145	0.010	0.036	0.021	0.021	0.055
31	0.080	-----	0.080	0.109	-----	0.426	-----	0.010	-----	0.021	0.021	-----
Maks.	0.187	0.599	0.109	0.187	0.426	1.18	0.508	0.358	0.080	0.055	0.036	0.187
Min.	0.036	0.055	0.055	0.055	0.109	0.237	0.145	0.010	0.003	0.010	0.021	0.021
Ortalama	0.045	0.095	0.061	0.081	0.133	0.460	0.315	0.089	0.005	0.031	0.021	0.044
LT/SN/Km2	0.292	0.619	0.396	0.527	0.868	3.00	2.06	0.584	0.032	0.205	0.137	0.288
AKIM mm.	0.783	1.61	1.06	1.41	2.10	8.05	5.34	1.56	0.084	0.548	0.368	0.745
MİL. M3	0.120	0.246	0.162	0.216	0.321	1.23	0.817	0.239	0.013	0.084	0.056	0.114

SU YILI (2006) YILLIK TOPLAM AKIM 3.62 MİLYON M3 24 MM. 0.8 LT/SN/Km2

15. Kizilirmak Havzasi

D15A289 GÖKSU DERESİ EĞERCİ

YERİ : **SİVAS GEMEREK İLÇESİ EĞERCİ BELDESİNDEDİR**
35°58'4" Doğu - 39°14'37" Kuzey

YAĞIŞ ALANI : **488,50 km2** **YAKLAŞIK KOT : 1150 m**

GÖZLEM SÜRESİ : **01.10.1999 - 30.09.2006**

ORTALAMA AKIMLAR : **Gözlem süresinde 3.296 m3/sn. (6 Yıllık) 2006 Su yılında 2.107 m3/sn.**

ANLIK EN ÇOK VE EN AZ AKIMLAR:

2006 Su yılında anlık ençok akım	**:**	**6.07**	**m3/sn**	**16.05.2006**
2006 Su yılında anlık enaz akım	**:**	**0.165**	**m3/sn**	**26.05.2006**
Gözlem süresinde anlık ençok akım	**:**	**17.6**	**m3/sn**	**05.03.2004**
Gözlem süresinde anlık enaz akım	**:**	**0.165**	**m3/sn**	**26.05.2006**

Akımlar 01 Ekim 2005 'den 30 Eylül 2006' a kadar m3/sn olarak

Gün	Ekim	Kasım	Aralık	Ocak	Şubat	Mart	Nisan	Mayıs	Haziran	Temmuz	Ağustos	Eylül
01	2.45	2.55	2.27	2.11	2.11	2.55	4.24	4.38	2.35	2.55	0.605	0.345
02	2.45	2.55	2.19	2.11	2.19	2.55	4.38	4.24	2.11	2.45	0.560	1.09
03	1.48	2.55	2.19	2.03	2.27	2.55	4.52	4.24	2.03	1.63	0.605	1.09
04	1.09	2.55	2.19	2.03	2.27	2.75	4.52	4.24	1.87	1.21	0.700	0.520
05	1.09	2.65	2.19	2.03	2.27	2.75	4.66	4.24	1.79	1.21	1.63	0.285
06	1.09	2.55	2.19	2.19	2.27	2.75	4.66	4.24	1.87	1.48	1.55	0.285
07	1.41	2.55	2.11	2.19	2.27	2.85	4.66	4.10	1.95	1.48	0.520	0.285
08	2.45	2.45	2.35	2.19	2.35	2.85	4.66	4.38	1.87	1.55	0.285	0.285
09	2.35	2.55	2.27	2.19	2.35	3.10	4.80	4.24	1.71	1.41	0.285	0.285
10	1.35	2.65	2.27	2.03	2.35	3.10	4.80	4.24	1.63	1.21	0.285	0.285
11	1.09	2.55	2.27	2.19	2.35	3.10	4.80	4.10	1.48	1.09	0.285	0.285
12	1.15	2.55	2.27	2.19	2.35	3.23	4.80	4.10	1.41	1.15	0.285	0.285
13	1.41	2.55	2.27	2.19	2.35	3.23	4.94	4.10	1.28	0.910	0.285	0.285
14	1.87	2.55	2.19	2.11	2.35	3.23	4.80	4.10	1.15	0.650	0.285	0.285
15	2.27	2.45	2.27	2.11	2.27	3.23	4.80	3.98	1.15	0.650	0.285	0.285
16	2.27	2.45	2.19	2.11	2.35	3.23	4.80	3.98	1.09	0.650	0.285	0.285
17	2.45	2.55	2.19	2.19	2.35	3.48	4.38	4.10	1.09	0.650	0.285	0.345
18	2.27	2.55	2.19	2.19	2.27	3.48	3.73	3.98	1.03	0.560	0.345	0.450
19	2.35	2.55	2.19	2.11	2.35	3.48	3.60	3.98	1.03	0.520	0.285	0.560
20	2.35	2.55	2.11	2.19	2.45	3.60	3.60	3.60	1.09	0.560	0.285	0.605
21	2.27	2.45	2.19	2.19	2.35	3.60	3.85	3.35	1.03	0.650	0.285	0.410
22	2.35	2.35	2.19	2.11	2.35	3.60	3.98	3.23	1.09	0.560	0.285	0.375
23	2.75	2.27	2.19	2.19	2.35	3.73	4.10	2.03	1.09	0.650	0.285	0.410
24	2.45	2.27	2.19	2.19	2.35	3.73	4.10	0.700	1.28	0.605	0.285	0.492
25	2.55	2.19	2.19	2.19	2.35	3.85	4.10	0.345	2.65	0.605	0.285	0.492
26	2.55	2.27	2.11	2.19	2.35	3.98	3.98	0.285	2.55	0.605	0.285	0.650
27	2.45	2.27	2.11	2.11	2.35	3.98	3.98	0.375	1.35	0.605	0.285	0.605
28	2.45	2.19	2.11	2.11	2.45	3.98	4.10	0.315	0.850	0.605	0.285	0.605
29	2.55	2.19	2.11	2.11	-----	4.10	4.10	0.285	1.55	0.605	0.285	0.700
30	2.55	2.19	2.03	2.11	-----	4.10	4.24	0.260	1.87	0.700	0.285	0.850
31	2.55	-----	2.11	2.11	-----	4.10	-----	0.185	-----	0.650	0.285	-----
Maks.	3.10	3.48	4.10	3.23	2.55	5.36	5.88	6.07	2.65	2.75	1.79	1.41
Min.	0.750	0.850	0.700	0.750	2.03	2.35	1.71	0.165	0.850	0.520	0.285	0.285
Ortalama	2.07	2.45	2.19	2.14	2.32	3.35	4.36	3.03	1.54	0.981	0.422	0.467
LT/SN/Km2	4.24	5.02	4.48	4.38	4.76	6.86	8.92	6.20	3.16	2.01	0.863	0.956
AKIM mm.	11.3	13.0	12.0	11.7	11.5	18.4	23.1	16.6	8.19	5.38	2.31	2.48
MİL. M3	5.54	6.35	5.87	5.73	5.62	8.97	11.3	8.11	4.00	2.63	1.13	1.21

SU YILI (2006) YILLIK TOPLAM AKIM 66.46 MİLYON M3 136 MM. 4.3 LT/SN/Km2

15. Kizilirmak Havzasi

D15A290 KIZILIRMAK DİKMENCİK

YERİ : **SİVAS MERKEZ KIZILKAVRAZ KÖPRÜSÜNDEDİR**
36°48'28" Doğu - 39°42'29" Kuzey

YAĞIŞ ALANI : **4262,00 km2** **YAKLAŞIK KOT : 1315 m**

GÖZLEM SÜRESİ : **01.10.1999 - 30.09.2006**

ORTALAMA AKIMLAR : **Gözlem süresinde 21.377 m3/sn. (7 Yıllık) 2006 Su yılında 32.905 m3/sn.**

ANLIK EN ÇOK VE EN AZ AKIMLAR:

2006 Su yılında anlık ençok akım	:	**254.**	**m3/sn**	**03.05.2006**
2006 Su yılında anlık enaz akım	:	**2.80**	**m3/sn**	**01.10.2005**
Gözlem süresinde anlık ençok akım	:	**360.**	**m3/sn**	**06.03.2004**
Gözlem süresinde anlık enaz akım	:	**1.36**	**m3/sn**	**22.11.2001**

Akımlar 01 Ekim 2005 'den 30 Eylül 2006' a kadar m3/sn olarak

Gün	Ekim	Kasım	Aralık	Ocak	Şubat	Mart	Nisan	Mayıs	Haziran	Temmuz	Ağustos	Eylül
01	3.00	6.16	7.64	8.06	20.0	23.0	141.	191.	44.2	15.9	5.20	3.60
02	3.00	6.80	7.64	4.88	20.0	31.3	178.	168.	41.6	14.5	5.20	3.60
03	3.00	7.22	7.64	3.92	24.0	34.6	189.	212.	40.3	13.8	5.20	3.60
04	3.20	7.22	7.64	3.60	26.0	45.5	147.	180.	39.0	13.1	4.88	3.60
05	3.40	8.90	7.64	3.40	26.0	44.2	121.	155.	37.9	12.4	4.88	3.60
06	3.40	13.1	7.64	5.52	27.0	41.6	111.	145.	36.8	12.4	4.88	3.60
07	3.20	10.2	7.22	7.64	27.0	46.8	104.	180.	35.7	13.8	4.56	3.60
08	3.20	9.32	7.22	8.90	29.1	77.2	102.	182.	34.6	13.8	4.24	3.60
09	3.20	8.48	7.22	8.90	22.0	125.	124.	184.	34.6	13.1	4.24	3.60
10	3.20	8.06	6.80	8.48	11.0	102.	155.	150.	29.1	11.7	4.24	3.60
11	3.20	7.64	6.80	8.06	11.0	71.6	160.	127.	27.0	11.0	3.92	3.60
12	3.20	7.22	6.80	7.64	12.4	56.2	147.	112.	25.0	11.0	3.92	3.92
13	3.00	6.80	6.80	7.64	14.5	50.7	127.	104.	24.0	9.74	3.92	3.92
14	5.20	6.48	6.80	7.64	14.5	54.8	125.	102.	23.0	8.06	3.92	3.92
15	4.88	6.48	6.80	6.80	13.8	73.0	118.	95.4	23.0	7.64	3.60	3.92
16	4.88	6.16	6.80	5.52	12.4	89.8	124.	89.8	22.0	7.64	3.60	3.92
17	5.52	6.16	7.22	4.24	10.6	71.6	108.	99.6	21.0	7.22	3.92	4.24
18	9.74	5.84	7.22	4.56	9.74	68.8	89.8	94.0	21.0	6.80	3.92	4.24
19	8.48	6.16	7.22	4.88	8.48	63.2	78.6	87.0	19.0	6.80	3.92	4.24
20	12.4	5.84	10.2	5.52	11.0	60.4	70.2	80.0	19.0	6.48	3.92	4.24
21	9.74	5.84	13.8	5.84	11.0	54.8	71.6	75.8	18.0	6.48	3.92	4.24
22	8.48	7.64	11.7	5.84	10.6	53.4	67.4	74.4	16.6	6.16	3.92	4.88
23	7.64	8.90	10.2	9.74	10.2	56.2	61.8	71.6	15.9	6.16	3.92	4.88
24	7.22	8.06	10.2	21.0	10.2	60.4	89.8	68.8	14.5	6.16	3.92	4.88
25	6.80	8.06	9.32	22.0	12.4	107.	150.	67.4	14.5	5.84	3.60	4.88
26	6.48	8.06	8.90	25.0	13.8	214.	133.	59.0	13.8	5.84	3.92	4.88
27	6.16	7.64	8.90	25.0	17.3	164.	99.6	52.0	13.1	5.52	3.92	5.20
28	5.52	7.64	8.90	24.0	21.0	130.	85.6	53.4	13.1	5.52	3.60	5.20
29	5.52	7.64	8.90	24.0	-----	115.	77.2	50.7	15.2	5.52	3.60	5.20
30	5.52	7.64	8.90	22.0	-----	108.	118.	48.1	16.6	5.52	3.60	4.88
31	5.52	-----	8.90	22.0	-----	115.	-----	46.8	-----	5.20	3.60	-----
Maks.	15.9	15.2	15.9	27.0	32.4	252.	224.	254.	48.1	19.0	5.52	5.20
Min.	2.80	5.84	6.48	3.20	8.06	21.0	57.6	45.5	12.4	5.20	3.60	3.40
Ortalama	5.38	7.58	8.24	10.7	16.3	77.7	116.	110.	25.0	9.06	4.12	4.18
LT/SN/Km2	1.26	1.78	1.93	2.51	3.83	18.2	27.2	25.8	5.86	2.13	0.966	0.980
AKIM mm.	3.38	4.61	5.18	6.73	9.26	48.8	70.4	69.0	15.2	5.69	2.59	2.54
MİL. M3	14.4	19.6	22.1	28.7	39.5	208.	300.	294.	64.7	24.3	11.0	10.8

SU YILI (2006) YILLIK TOPLAM AKIM 1037.10 MİLYON M3 243 MM. 7.7 LT/SN/Km2

15. Kizilirmak Havzasi

D15A292 ÖZDERE FELAHİYE

YERİ : **FELAHİYE-KAYAPINAR KASABASININ 2 KM KUZEY-DOĞSUNDADIR.**
35°38'2" Doğu - 39°7'29" Kuzey

YAĞIŞ ALANI : **73,00 km2** **YAKLAŞIK KOT : 1371 m**

GÖZLEM SÜRESİ : **01.12.1999 - 30.09.2006**

ORTALAMA AKIMLAR : **Gözlem süresinde 0.106 m3/sn. (6 Yıllık) 2006 Su yılında 0.072 m3/sn.**

ANLIK EN ÇOK VE EN AZ AKIMLAR:

2006 Su yılında anlık ençok akım	**:**	**0.369 m3/sn**	**21.05.2006**
2006 Su yılında anlık enaz akım	**:**	**0.003 m3/sn**	**01.10.2005**
Gözlem süresinde anlık ençok akım	**:**	**9.70 m3/sn**	**05.03.2004**
Gözlem süresinde anlık enaz akım	**:**	**0.001 m3/sn**	**16.08.2001**

2. Anahtar Eğrisi (Seviyeler cm olarak)

Akımlar 01 Ekim 2005 'den 30 Eylül 2006' a kadar m3/sn olarak

Gün	Ekim	Kasım	Aralık	Ocak	Şubat	Mart	Nisan	Mayıs	Haziran	Temmuz	Ağustos	Eylül
01	0.003	0.023	0.084	0.084	0.084	0.102	0.120	0.220	0.084	0.010	0.010	0.010
02	0.003	0.023	0.084	0.084	0.084	0.102	0.120	0.270	0.084	0.010	0.010	0.010
03	0.005	0.023	0.084	0.084	0.084	0.220	0.120	0.270	0.023	0.010	0.010	0.010
04	0.004	0.023	0.084	0.102	0.066	0.220	0.120	0.270	0.017	0.010	0.010	0.010
05	0.004	0.030	0.084	0.084	0.084	0.220	0.120	0.270	0.017	0.010	0.010	0.010
06	0.004	0.030	0.084	0.084	0.084	0.220	0.120	0.270	0.017	0.010	0.010	0.010
07	0.010	0.030	0.084	0.084	0.084	0.220	0.120	0.270	0.017	0.010	0.010	0.010
08	0.010	0.048	0.084	0.084	0.084	0.220	0.120	0.270	0.010	0.010	0.010	0.010
09	0.010	0.066	0.084	0.084	0.102	0.220	0.120	0.220	0.010	0.010	0.010	0.010
10	0.010	0.066	0.084	0.084	0.120	0.120	0.120	0.220	0.010	0.010	0.010	0.010
11	0.010	0.066	0.084	0.084	0.120	0.120	0.120	0.220	0.010	0.010	0.010	0.010
12	0.010	0.066	0.084	0.084	0.102	0.120	0.120	0.220	0.010	0.010	0.010	0.010
13	0.010	0.066	0.084	0.084	0.084	0.120	0.120	0.220	0.010	0.010	0.010	0.010
14	0.010	0.066	0.084	0.084	0.084	0.102	0.120	0.220	0.010	0.010	0.010	0.010
15	0.010	0.066	0.084	0.084	0.084	0.102	0.120	0.220	0.010	0.010	0.010	0.010
16	0.010	0.066	0.084	0.084	0.084	0.102	0.120	0.220	0.010	0.010	0.010	0.010
17	0.010	0.066	0.084	0.084	0.084	0.102	0.120	0.220	0.010	0.010	0.010	0.010
18	0.010	0.066	0.084	0.084	0.084	0.120	0.120	0.220	0.010	0.010	0.010	0.010
19	0.010	0.066	0.084	0.066	0.102	0.120	0.120	0.220	0.010	0.010	0.010	0.010
20	0.010	0.066	0.084	0.066	0.102	0.102	0.120	0.220	0.010	0.010	0.010	0.010
21	0.010	0.066	0.084	0.066	0.102	0.102	0.170	0.120	0.010	0.010	0.010	0.010
22	0.010	0.084	0.084	0.066	0.102	0.102	0.270	0.120	0.010	0.010	0.010	0.010
23	0.010	0.084	0.084	0.084	0.102	0.102	0.270	0.048	0.010	0.010	0.010	0.010
24	0.010	0.084	0.084	0.084	0.102	0.102	0.270	0.066	0.010	0.010	0.010	0.010
25	0.017	0.084	0.084	0.084	0.102	0.120	0.270	0.084	0.010	0.010	0.010	0.010
26	0.023	0.084	0.084	0.084	0.102	0.120	0.270	0.084	0.010	0.010	0.010	0.010
27	0.023	0.084	0.084	0.066	0.102	0.120	0.270	0.084	0.010	0.010	0.010	0.010
28	0.023	0.084	0.084	0.066	0.102	0.120	0.270	0.084	0.010	0.010	0.010	0.010
29	0.023	0.084	0.084	0.066	-----	0.120	0.270	0.084	0.010	0.010	0.010	0.010
30	0.023	0.084	0.084	0.066	-----	0.120	0.270	0.084	0.030	0.010	0.010	0.010
31	0.023	-----	0.084	0.066	-----	0.120	-----	0.084	-----	0.010	0.010	-----
Maks.	0.102	0.084	0.084	0.120	0.120	0.220	0.319	0.369	0.084	0.010	0.010	0.010
Min.	0.003	0.023	0.084	0.066	0.066	0.102	0.120	0.048	0.010	0.010	0.010	0.010
Ortalama	0.012	0.061	0.084	0.079	0.094	0.136	0.167	0.184	0.017	0.010	0.010	0.010
LT/SN/Km2	0.158	0.842	1.15	1.09	1.28	1.87	2.28	2.52	0.232	0.137	0.137	0.137
AKIM mm.	0.424	2.18	3.08	2.91	3.10	5.00	5.92	6.74	0.602	0.367	0.367	0.355
MİL. M3	0.031	0.159	0.225	0.213	0.227	0.365	0.432	0.492	0.044	0.027	0.027	0.026

SU YILI (2006) YILLIK TOPLAM AKIM 2.27 MİLYON M3 31 MM. 1.0 LT/SN/Km2

15. Kizilirmak Havzasi

D15A294 ÖZDERESİ HAZARŞAH

YERİ : **KAYSERİ MALATYA KARA YOLUNUN 50.KM SİNDEN SOLA HAZARŞAH TACİN KÖYLERİ YOLUNA GİRİLİR HAZARŞAH KÖYÜ ÇIKIŞI 200M SONRA SOLDA YOLA 100M MESAFEDEDİR ÖZDERE ÜZERİNDEDİR. 35°59'26" Doğu - 38°47'37" Kuzey**

YAĞIŞ ALANI : **20,50 km2** **YAKLAŞIK KOT : 1520 m**

GÖZLEM SÜRESİ : **01.10.1998 - 30.09.2006**

ORTALAMA AKIMLAR : **Gözlem süresinde 0.029 m3/sn. (6 Yıllık) 2006 Su yılında 0.023 m3/sn.**

ANLIK EN ÇOK VE EN AZ AKIMLAR:

2006 Su yılında anlık ençok akım	**:**	**0.200 m3/sn**	**03.05.2006**
2006 Su yılında anlık enaz akım	**:**	**0.000 m3/sn**	**01.10.2005**
Gözlem süresinde anlık ençok akım	**:**	**1.80 m3/sn**	**05.03.2004**
Gözlem süresinde anlık enaz akım	**:**	**0.000 m3/sn**	**22.08.2005**

İstasyon için kullanılmış anahtar bulunamadı.

Akımlar 01 Ekim 2005 'den 30 Eylül 2006' a kadar m3/sn olarak

Gün	Ekim	Kasım	Aralık	Ocak	Şubat	Mart	Nisan	Mayıs	Haziran	Temmuz	Ağustos	Eylül
01	0.004	0.004	0.009	0.004	0.001	0.001	0.050	0.100	0.050	0.004	0.004	0.009
02	0.004	0.009	0.009	0.004	0.004	0.001	0.050	0.130	0.050	0.004	0.004	0.009
03	0.004	0.009	0.009	0.004	0.004	0.001	0.050	0.130	0.023	0.004	0.004	0.009
04	0.004	0.009	0.009	0.004	0.001	0.004	0.065	0.200	0.023	0.004	0.004	0.009
05	0.004	0.009	0.009	0.004	0.001	0.004	0.065	0.200	0.023	0.004	0.004	0.009
06	0.004	0.009	0.009	0.004	0.001	0.004	0.065	0.200	0.023	0.004	0.004	0.009
07	0.004	0.009	0.009	0.004	0.004	0.004	0.065	0.200	0.023	0.004	0.004	0.009
08	0.004	0.009	0.009	0.004	0.004	0.004	0.065	0.200	0.023	0.004	0.004	0.009
09	0.004	0.009	0.009	0.001	0.004	0.001	0.065	0.200	0.023	0.004	0.004	0.009
10	0.004	0.009	0.009	0.001	0.004	0.001	0.065	0.160	0.023	0.004	0.004	0.009
11	0.004	0.009	0.009	0.001	0.004	0.001	0.065	0.160	0.023	0.009	0.004	0.009
12	0.004	0.009	0.009	0.001	0.004	0.001	0.065	0.160	0.023	0.009	0.004	0.009
13	0.004	0.009	0.009	0.001	0.004	0.004	0.065	0.130	0.023	0.009	0.004	0.009
14	0.004	0.009	0.009	0.001	0.004	0.004	0.065	0.130	0.015	0.009	0.004	0.009
15	0.004	0.009	0.009	0.001	0.004	0.004	0.065	0.100	0.015	0.009	0.004	0.009
16	0.004	0.009	0.009	0.001	0.004	0.004	0.065	0.100	0.015	0.009	0.004	0.009
17	0.004	0.009	0.009	0.001	0.004	0.004	0.065	0.085	0.015	0.009	0.004	0.009
18	0.004	0.009	0.009	0.001	0.004	0.009	0.065	0.085	0.015	0.009	0.004	0.009
19	0.004	0.009	0.009	0.001	0.004	0.015	0.065	0.085	0.015	0.009	0.004	0.009
20	0.004	0.009	0.009	0.001	0.004	0.015	0.065	0.085	0.009	0.009	0.004	0.009
21	0.004	0.009	0.004	0.001	0.004	0.015	0.065	0.085	0.009	0.004	0.004	0.004
22	0.004	0.009	0.004	0.001	0.004	0.023	0.065	0.085	0.009	0.004	0.004	0.004
23	0.004	0.009	0.004	0.001	0.004	0.023	0.065	0.085	0.004	0.004	0.004	0.004
24	0.004	0.009	0.004	0.001	0.004	0.023	0.065	0.085	0.004	0.004	0.004	0.004
25	0.004	0.009	0.004	0.001	0.004	0.036	0.160	0.085	0.004	0.004	0.004	0.004
26	0.004	0.009	0.004	0.001	0.004	0.065	0.130	0.085	0.004	0.004	0.004	0.004
27	0.004	0.009	0.004	0.001	0.004	0.065	0.130	0.065	0.004	0.004	0.004	0.004
28	0.004	0.009	0.004	0.001	0.004	0.050	0.130	0.065	0.004	0.004	0.004	0.004
29	0.004	0.009	0.004	0.001	-----	0.050	0.130	0.050	0.004	0.004	0.004	0.004
30	0.004	0.009	0.004	0.001	-----	0.050	0.130	0.050	0.004	0.004	0.004	0.004
31	0.004	-----	0.004	0.001	-----	0.050	-----	0.050	-----	0.004	0.004	-----
Maks.	0.004	0.009	0.085	0.004	0.004	0.065	0.160	0.200	0.050	0.009	0.009	0.009
Min.	KURU	0.004	KURU	0.001	0.001	0.001	0.050	0.050	0.004	0.004	0.004	0.004
Ortalama	0.004	0.009	0.007	0.002	0.004	0.017	0.077	0.117	0.017	0.006	0.004	0.007
LT/SN/Km2	0.195	0.431	0.352	0.087	0.174	0.843	3.78	5.71	0.816	0.274	0.195	0.358
AKIM mm.	0.523	1.12	0.944	0.232	0.421	2.26	9.80	15.3	2.12	0.733	0.523	0.927
MİL. M3	0.011	0.023	0.019	0.005	0.009	0.046	0.201	0.314	0.043	0.015	0.011	0.019

SU YILI (2006) YILLIK TOPLAM AKIM 0.72 MİLYON M3 35 MM. 1.1 LT/SN/Km2

15. Kizilirmak Havzasi

D15A295 HACILAR D. BEYKÖY

YERİ : **SAMSUN-ANKARA KARAYOLUNUN BEKDİĞİN BELDESİ SAPAĞINDAN 10 KM SONRA BEYKÖY'E ULAŞILIR BEYKÖY-ÇAMYATAĞI YOLUNUN 25 KM HACILAR DERESİ ÜZERİNDEDİR. 25 LİK PAFTADAKİ YERİ: F35-C4**

35°46'19" Doğu - 41°5'27" Kuzey

YAĞIŞ ALANI : **66,80 km2** **YAKLAŞIK KOT : 630 m**

GÖZLEM SÜRESİ : **01.01.2001 - 30.09.2006**

ORTALAMA AKIMLAR : **Gözlem süresinde 0.312 m3/sn. (3 Yıllık) 2006 Su yılında 0.225 m3/sn.**

ANLIK EN ÇOK VE EN AZ AKIMLAR:

2006 Su yılında anlık ençok akım	:	**4.15**	**m3/sn**	**26.02.2006**
2006 Su yılında anlık enaz akım	:	**0.002**	**m3/sn**	**31.08.2006**
Gözlem süresinde anlık ençok akım	:	**11.2**	**m3/sn**	**17.12.2003**
Gözlem süresinde anlık enaz akım	:	**0.000**	**m3/sn**	**25.09.2002**

3. Anahtar Eğrisi (Seviyeler cm olarak)

Seviye	Akım	Seviye	Akım	Seviye	Akım	Seviye	Akım
5	0.000	16	0.050	32	0.900	60	4.3
7	0.001	18	0.090	35	1.2	70	5.6
10	0.006	21	0.180	40	1.8	80	7.3
12	0.014	23	0.280	46	2.4	90	8.8
14	0.028	28	0.580	54	3.5	100	11.5

Akımlar 01 Ekim 2005 'den 30 Eylül 2006' a kadar m3/sn olarak

Gün	Ekim	Kasım	Aralık	Ocak	Şubat	Mart	Nisan	Mayıs	Haziran	Temmuz	Ağustos	Eylül
01	0.014	0.028	0.090	0.090	0.090	2.34	0.720	0.220	0.180	0.050	0.028	0.002
02	0.014	0.028	0.090	0.090	0.090	1.80	0.580	0.220	0.180	0.039	0.028	0.004
03	0.014	0.039	0.090	0.090	0.090	1.67	0.510	0.180	0.180	0.039	0.028	0.004
04	0.014	0.039	0.090	0.113	0.090	1.20	0.440	0.180	0.135	0.039	0.028	0.004
05	0.014	0.068	0.090	0.113	0.113	0.810	0.440	0.180	0.135	0.039	0.020	0.004
06	0.014	0.068	0.090	0.135	0.113	0.810	0.370	0.180	0.135	0.039	0.020	0.004
07	0.014	0.068	0.090	0.220	0.113	0.810	0.325	0.180	0.135	0.039	0.020	0.002
08	0.014	0.050	0.068	0.220	0.135	0.810	0.280	0.180	0.180	0.039	0.020	0.002
09	0.014	0.050	0.068	0.180	0.135	0.810	1.00	0.180	0.325	0.039	0.020	0.002
10	0.014	0.039	0.050	0.135	0.135	0.510	1.31	0.180	0.280	0.039	0.020	0.002
11	0.014	0.039	0.050	0.113	0.580	0.440	0.810	0.180	0.220	0.039	0.006	0.002
12	0.014	0.039	0.050	0.113	0.650	0.440	0.580	0.180	0.180	0.039	0.004	0.002
13	0.014	0.028	0.050	0.113	0.440	0.440	0.510	0.180	0.135	0.039	0.004	0.002
14	0.014	0.028	0.050	0.113	0.325	0.440	0.510	0.180	0.180	0.039	0.004	0.002
15	0.014	0.028	0.050	0.113	0.280	0.440	0.440	0.135	0.135	0.028	0.004	0.002
16	0.014	0.028	0.050	0.090	0.180	0.440	0.440	0.135	0.135	0.028	0.004	0.002
17	0.020	0.028	0.050	0.090	0.180	0.440	0.370	0.440	0.135	0.028	0.004	0.002
18	0.028	0.039	0.050	0.090	0.220	0.370	0.370	0.900	0.113	0.028	0.004	0.002
19	0.028	0.068	0.068	0.090	0.510	0.440	0.325	0.510	0.113	0.028	0.004	0.002
20	0.028	0.068	0.068	0.090	0.810	0.510	0.325	0.325	0.113	0.028	0.004	0.002
21	0.028	0.090	0.068	0.090	0.900	0.650	0.325	0.280	0.113	0.028	0.004	0.002
22	0.028	0.135	0.068	0.090	1.00	0.810	0.280	0.220	0.090	0.028	0.004	0.002
23	0.028	0.135	0.068	0.090	1.00	0.650	0.280	0.180	0.113	0.028	0.004	0.002
24	0.028	0.113	0.068	0.090	1.20	0.510	0.280	0.180	0.090	0.028	0.004	0.002
25	0.028	0.113	0.068	0.090	2.00	0.510	0.280	0.220	0.090	0.028	0.004	0.002
26	0.028	0.113	0.068	0.090	2.83	0.720	0.280	0.220	0.090	0.028	0.004	0.002
27	0.028	0.135	0.068	0.090	2.45	1.54	0.280	1.20	0.090	0.028	0.004	0.002
28	0.028	0.113	0.068	0.090	2.00	1.90	0.220	0.810	0.068	0.028	0.004	0.002
29	0.028	0.090	0.068	0.090	-----	1.67	0.220	0.440	0.068	0.028	0.004	0.002
30	0.028	0.090	0.068	0.090	-----	1.20	0.220	0.325	0.090	0.028	0.004	0.002
31	0.028	-----	0.090	0.090	-----	0.900	-----	0.220	-----	0.028	0.002	-----
Maks.	0.039	0.650	0.090	0.280	4.15	2.83	2.70	2.45	2.34	0.090	0.028	0.006
Min.	0.014	0.028	0.039	0.090	0.090	0.370	0.220	0.113	0.050	0.028	0.002	0.002
Ortalama	0.021	0.067	0.068	0.109	0.666	0.872	0.444	0.301	0.141	0.033	0.010	0.002
LT/SN/Km2	0.307	0.997	1.02	1.64	9.98	13.1	6.65	4.51	2.11	0.499	0.153	0.035
AKIM mm.	0.823	2.58	2.74	4.39	24.1	35.0	17.2	12.1	5.47	1.34	0.409	0.091
MİL. M3	0.055	0.173	0.183	0.293	1.61	2.34	1.15	0.807	0.365	0.089	0.027	0.006

SU YILI (2006) YILLIK TOPLAM AKIM 7.10 MİLYON M3 106 MM. 3.4 LT/SN/Km2

15. Kizilirmak Havzasi

D15A296 ASACAK DERESİ GEVREK

YERİ : YOZGAT-SORGUN-ÇEKEREK KARAYOLUNDAN ÇİĞDEMLİ KASABASINAGELİNİR.5 KM.SONRA SAĞDA GEVREK KÖYÜNE GİRMEDEN KÖPRÜNÜN 25 M. MENBASINDA BETON EŞİKLİDİR.
35°19'13" Doğu - 39°52'22" Kuzey

YAĞIŞ ALANI : 35,00 km2 **YAKLAŞIK KOT :** 1158 m

GÖZLEM SÜRESİ : 01.10.2001 - 30.09.2006

ORTALAMA AKIMLAR : Gözlem süresinde 0.082 m3/sn. (5 Yıllık) 2006 Su yılında 0.069 m3/sn.

ANLIK EN ÇOK VE EN AZ AKIMLAR:

2006 Su yılında anlık ençok akım	:	1.02	m3/sn	03.03.2006
2006 Su yılında anlık enaz akım	:	0.000	m3/sn	01.10.2005
Gözlem süresinde anlık ençok akım	:	3.50	m3/sn	03.04.2003
Gözlem süresinde anlık enaz akım	:	0.000	m3/sn	01.10.2001

2. Anahtar Eğrisi (Seviyeler cm olarak)

Seviye	Akım	Seviye	Akım	Seviye	Akım	Seviye	Akım
1	0.000	11	0.091	25	0.560	60	1.6
3	0.000	12	0.122	30	0.740	70	1.8
5	0.003	13	0.153	35	0.900	74	2.0
7	0.010	17	0.280	40	1.0	80	2.1
9	0.038	20	0.370	50	1.3	120	2.8

Akımlar 01 Ekim 2005 'den 30 Eylül 2006' a kadar m3/sn olarak

Gün	Ekim	Kasım	Aralık	Ocak	Şubat	Mart	Nisan	Mayıs	Haziran	Temmuz	Ağustos	Eylül
01	KURU	KURU	KURU	KURU	KURU	0.280	0.340	0.185	0.020	0.001	KURU	KURU
02	KURU	KURU	KURU	KURU	KURU	0.248	0.446	0.217	0.020	0.001	KURU	KURU
03	KURU	KURU	KURU	KURU	KURU	0.248	0.446	0.340	0.020	0.001	KURU	KURU
04	KURU	KURU	KURU	KURU	KURU	0.217	0.446	0.310	0.010	0.001	KURU	KURU
05	KURU	KURU	KURU	KURU	KURU	0.248	0.408	0.310	0.010	0.001	KURU	KURU
06	KURU	KURU	KURU	KURU	KURU	0.248	0.370	0.280	0.010	0.001	KURU	KURU
07	KURU	KURU	KURU	KURU	KURU	0.280	0.340	0.280	0.010	0.001	KURU	KURU
08	KURU	KURU	KURU	KURU	KURU	0.310	0.340	0.122	0.010	0.001	KURU	KURU
09	KURU	KURU	KURU	KURU	KURU	0.310	0.340	0.280	0.010	0.001	KURU	KURU
10	KURU	KURU	KURU	KURU	KURU	0.280	0.340	0.217	0.010	0.001	KURU	KURU
11	KURU	KURU	KURU	KURU	KURU	0.248	0.340	0.217	0.010	0.001	KURU	KURU
12	KURU	KURU	KURU	KURU	KURU	0.280	0.340	0.185	0.010	0.001	KURU	KURU
13	KURU	KURU	KURU	KURU	KURU	0.280	0.310	0.153	0.010	0.001	KURU	KURU
14	KURU	KURU	KURU	KURU	KURU	0.280	0.310	0.153	0.010	0.001	KURU	KURU
15	KURU	KURU	KURU	KURU	KURU	0.280	0.340	0.153	0.001	0.001	KURU	KURU
16	KURU	KURU	KURU	KURU	KURU	0.310	0.340	0.153	0.001	0.001	KURU	KURU
17	KURU	KURU	KURU	KURU	KURU	0.310	0.340	0.153	0.001	KURU	KURU	KURU
18	KURU	KURU	KURU	KURU	KURU	0.310	0.310	0.153	0.001	KURU	KURU	KURU
19	KURU	KURU	KURU	KURU	KURU	0.310	0.280	0.153	0.001	KURU	KURU	KURU
20	KURU	KURU	KURU	KURU	0.003	0.340	0.248	0.091	0.001	KURU	KURU	KURU
21	KURU	KURU	KURU	KURU	0.010	0.446	0.248	0.091	0.001	KURU	KURU	KURU
22	KURU	KURU	KURU	KURU	0.020	0.446	0.248	0.091	0.001	KURU	KURU	KURU
23	KURU	KURU	KURU	KURU	0.065	0.446	0.248	0.091	0.001	KURU	KURU	KURU
24	KURU	KURU	KURU	KURU	0.122	0.446	0.248	0.091	0.001	KURU	KURU	KURU
25	KURU	KURU	KURU	KURU	0.122	0.408	0.248	0.091	0.001	KURU	KURU	KURU
26	KURU	KURU	KURU	KURU	0.185	0.446	0.217	0.065	0.001	KURU	KURU	KURU
27	KURU	KURU	KURU	KURU	0.217	0.408	0.185	0.065	0.001	KURU	KURU	KURU
28	KURU	KURU	KURU	KURU	0.280	0.408	0.153	0.038	0.001	KURU	KURU	KURU
29	KURU	KURU	KURU	KURU	-----	0.370	0.153	0.020	0.001	KURU	KURU	KURU
30	KURU	KURU	KURU	KURU	-----	0.340	0.153	0.020	0.001	KURU	KURU	KURU
31	KURU	-----	KURU	KURU	-----	0.340	-----	0.020	-----	KURU	KURU	-----
Maks.	KURU	KURU	KURU	KURU	0.280	1.02	0.446	0.560	0.020	0.001	KURU	KURU
Min.	KURU	KURU	KURU	KURU	KURU	0.217	0.122	0.020	0.001	KURU	KURU	KURU
Ortalama	KURU	KURU	KURU	KURU	0.037	0.326	0.303	0.154	0.006	0.001	KURU	KURU
LT/SN/Km2	0.000	0.000	0.000	0.000	1.04	9.33	8.64	4.41	0.177	0.015	0.000	0.000
AKIM mm.	0.000	0.000	0.000	0.000	2.53	25.0	22.4	11.8	0.459	0.039	0.000	0.000
MİL. M3	0.000	0.000	0.000	0.000	0.088	0.874	0.784	0.414	0.016	0.001	0.000	0.000

SU YILI (2006) YILLIK TOPLAM AKIM 2.18 MİLYON M3 62 MM. 2.0 LT/SN/Km2

15. Kizilirmak Havzasi

D15A298 YONCALIK DERESİ EYNELLİ

YERİ : **YOZGAT-SARIKAYA-EYNELLİ ARA YOLUNDAN AKDAĞMADENİ NE GİDERKEN EYNELLİ KÖYÜ ÇIKIŞINDA 750 M.MESAFEDEDİR.BETON EŞİKLİ 35°43'50" Doğu - 39°34'26" Kuzey**

YAĞIŞ ALANI : **35,80 km2** **YAKLAŞIK KOT : 1400 m**

GÖZLEM SÜRESİ : **01.10.2001 - 30.09.2006**

ORTALAMA AKIMLAR : **Gözlem süresinde 0.130 m3/sn. (5 Yıllık) 2006 Su yılında 0.082 m3/sn.**

ANLIK EN ÇOK VE EN AZ AKIMLAR:

2006 Su yılında anlık ençok akım	**:**	**0.240 m3/sn**	**23.03.2006**
2006 Su yılında anlık enaz akım	**:**	**0.022 m3/sn**	**29.09.2006**
Gözlem süresinde anlık ençok akım	**:**	**3.44 m3/sn**	**21.08.2002**
Gözlem süresinde anlık enaz akım	**:**	**0.019 m3/sn**	**06.07.2005**

İstasyon için kullanılmış anahtar bulunamadı.

Akımlar 01 Ekim 2005 'den 30 Eylül 2006' a kadar m3/sn olarak

Gün	Ekim	Kasım	Aralık	Ocak	Şubat	Mart	Nisan	Mayıs	Haziran	Temmuz	Ağustos	Eylül
01	0.080	0.080	0.071	0.071	0.071	0.090	0.120	0.150	0.120	0.071	0.051	0.032
02	0.071	0.080	0.071	0.071	0.071	0.090	0.150	0.150	0.120	0.071	0.051	0.032
03	0.071	0.080	0.071	0.071	0.071	0.090	0.180	0.150	0.120	0.071	0.051	0.032
04	0.080	0.080	0.071	0.071	0.071	0.090	0.150	0.150	0.120	0.071	0.051	0.032
05	0.080	0.080	0.071	0.071	0.071	0.090	0.150	0.150	0.120	0.071	0.051	0.032
06	0.080	0.090	0.071	0.071	0.071	0.090	0.150	0.120	0.120	0.071	0.051	0.032
07	0.080	0.090	0.071	0.080	0.071	0.090	0.150	0.120	0.090	0.071	0.051	0.032
08	0.080	0.090	0.071	0.090	0.061	0.090	0.150	0.150	0.090	0.071	0.051	0.032
09	0.071	0.090	0.071	0.080	0.061	0.090	0.150	0.150	0.090	0.071	0.051	0.032
10	0.071	0.090	0.071	0.080	0.061	0.090	0.150	0.120	0.080	0.071	0.051	0.032
11	0.071	0.090	0.071	0.080	0.061	0.090	0.150	0.120	0.080	0.071	0.051	0.032
12	0.071	0.090	0.071	0.080	0.071	0.090	0.150	0.150	0.080	0.061	0.041	0.032
13	0.071	0.090	0.071	0.080	0.080	0.090	0.150	0.150	0.080	0.061	0.041	0.032
14	0.071	0.090	0.071	0.080	0.071	0.090	0.150	0.150	0.080	0.061	0.041	0.032
15	0.071	0.090	0.071	0.071	0.071	0.090	0.150	0.150	0.080	0.061	0.041	0.032
16	0.071	0.090	0.071	0.071	0.071	0.090	0.150	0.150	0.071	0.061	0.041	0.032
17	0.071	0.071	0.071	0.071	0.071	0.090	0.150	0.150	0.071	0.061	0.041	0.032
18	0.080	0.071	0.071	0.071	0.071	0.090	0.150	0.150	0.071	0.061	0.041	0.032
19	0.080	0.071	0.071	0.071	0.071	0.090	0.150	0.150	0.071	0.061	0.041	0.032
20	0.080	0.071	0.071	0.071	0.071	0.090	0.120	0.120	0.071	0.061	0.041	0.032
21	0.080	0.071	0.071	0.071	0.071	0.090	0.120	0.120	0.061	0.061	0.041	0.032
22	0.080	0.071	0.071	0.071	0.080	0.150	0.120	0.120	0.061	0.061	0.041	0.032
23	0.080	0.071	0.071	0.071	0.080	0.150	0.120	0.120	0.061	0.061	0.032	0.032
24	0.080	0.071	0.071	0.071	0.080	0.150	0.120	0.120	0.051	0.061	0.032	0.032
25	0.080	0.071	0.071	0.071	0.080	0.150	0.180	0.120	0.051	0.061	0.032	0.032
26	0.080	0.071	0.071	0.071	0.090	0.150	0.180	0.120	0.061	0.051	0.032	0.032
27	0.080	0.071	0.071	0.071	0.090	0.150	0.120	0.120	0.061	0.051	0.032	0.032
28	0.080	0.071	0.071	0.071	0.090	0.150	0.120	0.120	0.061	0.051	0.032	0.032
29	0.080	0.071	0.071	0.071	-----	0.150	0.120	0.120	0.071	0.051	0.032	0.022
30	0.080	0.071	0.071	0.071	-----	0.150	0.150	0.120	0.071	0.051	0.032	0.022
31	0.080	-----	0.071	0.071	-----	0.150	-----	0.120	-----	0.051	0.032	-----
Maks.	0.120	0.090	0.071	0.090	0.090	0.240	0.180	0.240	0.120	0.080	0.051	0.032
Min.	0.071	0.071	0.061	0.071	0.051	0.080	0.120	0.090	0.051	0.051	0.032	0.022
Ortalama	0.077	0.079	0.071	0.074	0.073	0.109	0.144	0.135	0.081	0.063	0.042	0.031
LT/SN/Km2	2.15	2.22	1.98	2.06	2.05	3.05	4.02	3.76	2.27	1.75	1.17	0.875
AKIM mm.	5.75	5.75	5.31	5.51	4.95	8.18	10.4	10.1	5.88	4.68	3.14	2.27
MİL. M3	0.206	0.206	0.190	0.197	0.177	0.293	0.373	0.360	0.210	0.168	0.112	0.081

SU YILI (2006) YILLIK TOPLAM AKIM 2.57 MİLYON M3 72 MM. 2.3 LT/SN/Km2

15. Kizilirmak Havzasi

D15A299 KURU DERE ARMUTLU

YERİ : **SİVAS MERKEZ ARMUTLU KÖYÜ İLE KARACAÖREN KÖYÜ ARASINDADIR**
37°17'16" Doğu - 39°34'38" Kuzey

YAĞIŞ ALANI : **3,85 km2** **YAKLAŞIK KOT : 1390 m**

GÖZLEM SÜRESİ : **01.10.2003 - 30.09.2006**

ORTALAMA AKIMLAR : **Gözlem süresinde 0.022 m3/sn. (3 Yıllık) 2006 Su yılında 0.032 m3/sn.**

ANLIK EN ÇOK VE EN AZ AKIMLAR:

2006 Su yılında anlık ençok akım	**:**	**8.43 m3/sn**	**04.05.2006**
2006 Su yılında anlık enaz akım	**:**	**0.001 m3/sn**	**20.01.2006**
Gözlem süresinde anlık ençok akım	**:**	**8.43 m3/sn**	**04.05.2006**
Gözlem süresinde anlık enaz akım	**:**	**0.001 m3/sn**	**01.10.2003**

Akımlar 01 Ekim 2005 'den 30 Eylül 2006' a kadar m3/sn olarak

Gün	Ekim	Kasım	Aralık	Ocak	Şubat	Mart	Nisan	Mayıs	Haziran	Temmuz	Ağustos	Eylül
01	0.012	0.020	0.012	0.012	0.003	0.105	0.074	0.105	0.032	0.012	0.012	0.006
02	0.012	0.020	0.012	0.006	0.003	0.105	0.074	0.215	0.032	0.012	0.012	0.006
03	0.074	0.020	0.012	0.006	0.003	0.105	0.105	0.155	0.032	0.012	0.012	0.006
04	0.020	0.020	0.012	0.012	0.003	0.074	0.074	0.215	0.032	0.012	0.012	0.006
05	0.020	0.074	0.012	0.012	0.006	0.050	0.074	0.155	0.032	0.012	0.012	0.006
06	0.020	0.032	0.012	0.020	0.006	0.050	0.074	0.105	0.032	0.012	0.012	0.006
07	0.020	0.020	0.012	0.020	0.020	0.050	0.074	0.074	0.032	0.012	0.012	0.006
08	0.012	0.020	0.012	0.020	0.032	0.050	0.074	0.074	0.032	0.012	0.012	0.006
09	0.012	0.020	0.012	0.020	0.050	0.074	0.050	0.074	0.020	0.012	0.012	0.006
10	0.012	0.020	0.012	0.020	0.032	0.074	0.050	0.074	0.020	0.012	0.006	0.006
11	0.012	0.020	0.012	0.020	0.032	0.074	0.050	0.050	0.020	0.012	0.006	0.006
12	0.012	0.020	0.012	0.020	0.050	0.074	0.050	0.050	0.020	0.012	0.006	0.006
13	0.012	0.020	0.012	0.012	0.074	0.074	0.050	0.050	0.020	0.012	0.006	0.006
14	0.012	0.020	0.012	0.012	0.050	0.050	0.050	0.050	0.020	0.012	0.006	0.006
15	0.012	0.012	0.012	0.012	0.032	0.074	0.050	0.032	0.020	0.012	0.006	0.006
16	0.032	0.012	0.020	0.006	0.074	0.050	0.050	0.050	0.020	0.012	0.006	0.006
17	0.032	0.012	0.020	0.006	0.105	0.050	0.050	0.050	0.020	0.012	0.006	0.006
18	0.032	0.012	0.012	0.006	0.032	0.050	0.050	0.050	0.020	0.012	0.006	0.006
19	0.074	0.012	0.012	0.006	0.020	0.050	0.032	0.050	0.020	0.012	0.006	0.006
20	0.020	0.012	0.020	0.001	0.012	0.050	0.032	0.032	0.020	0.012	0.006	0.006
21	0.020	0.012	0.020	0.003	0.032	0.050	0.032	0.032	0.020	0.012	0.006	0.006
22	0.020	0.012	0.020	0.003	0.032	0.050	0.032	0.032	0.012	0.012	0.006	0.006
23	0.020	0.012	0.012	0.003	0.032	0.050	0.105	0.032	0.012	0.012	0.006	0.006
24	0.012	0.012	0.020	0.003	0.032	0.050	0.387	0.032	0.012	0.012	0.006	0.006
25	0.012	0.012	0.020	0.003	0.032	0.155	0.387	0.032	0.012	0.012	0.006	0.006
26	0.012	0.012	0.020	0.003	0.050	0.155	0.105	0.032	0.012	0.012	0.006	0.006
27	0.012	0.012	0.012	0.003	0.074	0.155	0.105	0.032	0.012	0.012	0.006	0.012
28	0.012	0.012	0.012	0.003	0.074	0.105	0.074	0.032	0.012	0.012	0.006	0.012
29	0.020	0.012	0.012	0.003	-----	0.105	0.074	0.032	0.012	0.012	0.006	0.012
30	0.020	0.012	0.012	0.003	-----	0.105	0.301	0.032	0.020	0.012	0.006	0.012
31	0.020	-----	0.012	0.003	-----	0.074	-----	0.032	-----	0.012	0.006	-----
Maks.	1.67	0.887	0.020	0.074	0.387	1.01	5.89	8.43	0.301	0.012	0.012	0.473
Min.	0.006	0.012	0.006	0.001	0.003	0.032	0.032	0.032	0.012	0.012	0.006	0.006
Ortalama	0.021	0.018	0.014	0.009	0.036	0.077	0.093	0.067	0.021	0.012	0.008	0.007
LT/SN/Km2	5.40	4.66	3.65	2.36	9.25	20.0	24.1	17.3	5.47	3.12	2.01	1.77
AKIM mm.	14.5	12.1	9.78	6.33	22.4	53.6	62.6	46.3	14.2	8.35	5.39	4.58
MİL. M3	0.056	0.046	0.038	0.024	0.086	0.206	0.241	0.178	0.055	0.032	0.021	0.018

SU YILI (2006) YILLIK TOPLAM AKIM 1.00 MİLYON M3 260 MM. 8.2 LT/SN/Km2

15. Kizilirmak Havzasi

D15A300 TATLI DERE KARACAÖREN

YERİ : **SİVAS MERKEZ KARACAÖREN KÖYÜNDEDİR.**
37°18'7" Doğu - 39°34'25" Kuzey

YAĞIŞ ALANI : **11,51 km2** **YAKLAŞIK KOT : 1405 m**

GÖZLEM SÜRESİ : **01.10.2003 - 30.09.2006**

ORTALAMA AKIMLAR : **Gözlem süresinde 0.191 m3/sn. (2 Yıllık) 2006 Su yılında 0.227 m3/sn.**

ANLIK EN ÇOK VE EN AZ AKIMLAR:

2006 Su yılında anlık ençok akım	**:**	**7.19**	**m3/sn**	**04.05.2006**
2006 Su yılında anlık enaz akım	**:**	**0.000**	**m3/sn**	**01.10.2005**
Gözlem süresinde anlık ençok akım	**:**	**7.19**	**m3/sn**	**04.05.2006**
Gözlem süresinde anlık enaz akım	**:**	**0.000**	**m3/sn**	**01.10.2004**

Akımlar 01 Ekim 2005 'den 30 Eylül 2006' a kadar m3/sn olarak

Gün	Ekim	Kasım	Aralık	Ocak	Şubat	Mart	Nisan	Mayıs	Haziran	Temmuz	Ağustos	Eylül
01	KURU	0.228	0.228	0.077	0.077	0.266	0.612	1.54	2.70	0.153	KURU	KURU
02	KURU	0.228	0.153	0.077	0.077	0.266	0.612	1.77	1.54	0.115	KURU	KURU
03	0.266	0.228	0.153	0.077	0.077	0.266	0.380	1.08	0.844	0.115	KURU	KURU
04	0.304	0.228	0.153	0.077	0.039	0.304	0.380	1.77	0.380	0.115	KURU	KURU
05	0.266	0.304	0.153	0.077	0.039	0.304	0.380	1.08	0.380	0.115	KURU	KURU
06	0.077	0.266	0.153	0.077	0.039	0.304	0.342	1.08	0.304	0.115	KURU	KURU
07	KURU	0.266	0.153	0.077	0.039	0.304	0.342	0.612	0.228	0.115	KURU	KURU
08	0.039	0.266	0.153	0.115	0.039	0.304	0.612	0.612	0.228	0.115	KURU	KURU
09	KURU	0.266	0.153	0.153	0.191	0.304	1.31	0.612	0.153	0.153	KURU	KURU
10	KURU	0.266	0.153	0.077	0.228	0.266	1.08	0.380	0.228	0.115	KURU	KURU
11	KURU	0.266	0.153	0.115	0.191	0.266	0.612	0.380	0.228	0.115	KURU	KURU
12	KURU	0.228	0.153	0.077	0.191	0.266	0.612	0.612	0.228	0.077	KURU	KURU
13	KURU	0.191	0.153	0.077	0.228	0.266	0.612	0.380	0.191	0.077	KURU	KURU
14	KURU	0.191	0.077	0.077	0.266	0.266	0.380	0.342	0.153	0.115	KURU	KURU
15	KURU	0.191	0.153	0.077	0.228	0.304	0.612	0.342	0.153	0.001	KURU	KURU
16	0.077	0.191	0.153	0.077	0.228	0.304	0.380	0.380	0.153	KURU	KURU	KURU
17	0.266	0.191	0.153	0.077	0.191	0.266	0.380	0.342	0.153	KURU	KURU	KURU
18	0.266	0.191	0.153	0.077	0.266	0.266	0.342	0.342	0.153	KURU	KURU	KURU
19	0.266	0.191	0.153	0.077	0.266	0.266	0.342	0.342	0.153	KURU	KURU	KURU
20	0.266	0.191	0.191	0.077	0.266	0.266	0.342	0.304	0.115	KURU	KURU	KURU
21	0.266	0.191	0.153	0.077	0.228	0.266	0.342	0.304	0.115	KURU	KURU	KURU
22	0.266	0.191	0.153	0.077	0.191	0.266	0.342	0.304	0.115	KURU	KURU	KURU
23	0.266	0.153	0.077	0.077	0.191	0.266	0.612	0.304	0.115	KURU	KURU	KURU
24	0.266	0.115	0.153	0.077	0.191	0.342	2.24	0.304	0.115	KURU	KURU	KURU
25	0.228	0.153	0.115	0.077	0.266	1.08	1.31	0.304	0.115	KURU	KURU	KURU
26	0.228	0.153	0.115	0.077	0.266	0.612	0.844	0.304	0.115	KURU	KURU	KURU
27	0.228	0.153	0.115	0.077	0.266	0.380	0.844	0.304	0.115	KURU	KURU	KURU
28	0.228	0.153	0.115	0.077	0.266	0.380	0.612	0.304	0.115	KURU	KURU	KURU
29	0.228	0.153	0.115	0.077	-----	0.380	1.31	0.304	0.115	KURU	KURU	KURU
30	0.228	0.153	0.115	0.077	-----	0.342	1.31	0.304	0.153	KURU	KURU	KURU
31	0.228	-----	0.115	0.077	-----	0.380	-----	0.304	-----	KURU	KURU	-----
Maks.	0.844	0.342	0.228	0.153	0.380	2.24	5.30	7.19	2.70	0.153	KURU	KURU
Min.	KURU	KURU	KURU	0.001	0.039	0.266	0.342	0.228	0.115	KURU	KURU	KURU
Ortalama	0.153	0.205	0.143	0.082	0.180	0.333	0.681	0.569	0.328	0.052	KURU	KURU
LT/SN/Km2	13.3	17.8	12.4	7.12	15.6	28.9	59.2	49.5	28.5	4.52	0.000	0.000
AKIM mm.	35.7	46.1	33.3	19.1	37.8	77.5	153.	132.	74.0	12.1	0.000	0.000
MİL. M3	0.411	0.530	0.383	0.219	0.435	0.891	1.77	1.52	0.851	0.139	0.000	0.000

SU YILI (2006) YILLIK TOPLAM AKIM 7.15 MİLYON M3 621 MM. 19.7 LT/SN/Km2

15. Kizilirmak Havzasi

D15A301 GÖYNÜK DERE HAYRANLI

YERİ : **SİVAS MERKEZ HAYRANLI KÖYÜNDEDİR.**
36°51'7" Doğu - 39°47'32" Kuzey

YAĞIŞ ALANI : **3,07 km2** **YAKLAŞIK KOT : 1439 m**

GÖZLEM SÜRESİ : **01.10.2004 - 30.09.2006**

ORTALAMA AKIMLAR : **Gözlem süresinde 0.023 m3/sn. (2 Yıllık) 2006 Su yılında 0.028 m3/sn.**

ANLIK EN ÇOK VE EN AZ AKIMLAR:

2006 Su yılında anlık ençok akım	**:**	**0.090 m3/sn**	**05.05.2006**
2006 Su yılında anlık enaz akım	**:**	**0.018 m3/sn**	**28.10.2005**
Gözlem süresinde anlık ençok akım	**:**	**0.090 m3/sn**	**05.05.2006**
Gözlem süresinde anlık enaz akım	**:**	**0.003 m3/sn**	**12.01.2005**

Akımlar 01 Ekim 2005 'den 30 Eylül 2006' a kadar m3/sn olarak

Gün	Ekim	Kasım	Aralık	Ocak	Şubat	Mart	Nisan	Mayıs	Haziran	Temmuz	Ağustos	Eylül
01	0.025	0.018	0.018	0.018	0.018	0.018	0.033	0.051	0.041	0.033	0.033	0.033
02	0.025	0.018	0.018	0.018	0.018	0.018	0.033	0.051	0.041	0.033	0.033	0.033
03	0.025	0.018	0.018	0.018	0.018	0.018	0.033	0.051	0.041	0.033	0.033	0.033
04	0.025	0.018	0.018	0.018	0.018	0.025	0.033	0.051	0.033	0.033	0.033	0.033
05	0.025	0.025	0.018	0.018	0.018	0.025	0.033	0.051	0.033	0.033	0.033	0.033
06	0.025	0.025	0.018	0.018	0.018	0.025	0.033	0.051	0.033	0.033	0.033	0.033
07	0.025	0.025	0.018	0.018	0.018	0.025	0.033	0.051	0.033	0.033	0.033	0.033
08	0.025	0.025	0.018	0.018	0.018	0.025	0.033	0.051	0.033	0.033	0.033	0.033
09	0.025	0.025	0.018	0.018	0.018	0.025	0.033	0.051	0.033	0.033	0.033	0.033
10	0.025	0.025	0.018	0.018	0.018	0.025	0.033	0.051	0.033	0.033	0.033	0.033
11	0.025	0.025	0.018	0.018	0.018	0.025	0.033	0.051	0.033	0.033	0.033	0.033
12	0.025	0.025	0.018	0.018	0.018	0.025	0.033	0.041	0.033	0.033	0.033	0.033
13	0.025	0.025	0.018	0.018	0.018	0.025	0.033	0.041	0.033	0.033	0.033	0.033
14	0.025	0.025	0.018	0.018	0.018	0.025	0.033	0.041	0.033	0.033	0.033	0.033
15	0.025	0.025	0.018	0.018	0.018	0.025	0.033	0.041	0.033	0.033	0.033	0.033
16	0.033	0.025	0.018	0.018	0.018	0.025	0.033	0.041	0.033	0.033	0.033	0.033
17	0.033	0.025	0.018	0.018	0.018	0.025	0.033	0.041	0.033	0.033	0.033	0.033
18	0.033	0.025	0.018	0.018	0.018	0.025	0.033	0.041	0.033	0.033	0.033	0.033
19	0.025	0.025	0.018	0.018	0.018	0.025	0.033	0.041	0.033	0.033	0.033	0.033
20	0.025	0.025	0.018	0.018	0.018	0.025	0.033	0.041	0.033	0.033	0.033	0.033
21	0.025	0.025	0.018	0.018	0.018	0.025	0.033	0.041	0.033	0.033	0.033	0.033
22	0.025	0.025	0.018	0.018	0.018	0.025	0.033	0.041	0.033	0.033	0.033	0.033
23	0.025	0.025	0.018	0.018	0.018	0.025	0.033	0.041	0.033	0.033	0.033	0.033
24	0.025	0.025	0.018	0.018	0.018	0.025	0.033	0.041	0.033	0.033	0.033	0.033
25	0.025	0.018	0.018	0.018	0.018	0.033	0.041	0.041	0.033	0.033	0.033	0.033
26	0.025	0.018	0.018	0.018	0.018	0.033	0.041	0.041	0.033	0.033	0.033	0.033
27	0.025	0.018	0.018	0.018	0.018	0.033	0.041	0.041	0.033	0.033	0.033	0.033
28	0.018	0.018	0.018	0.018	0.018	0.033	0.041	0.041	0.033	0.033	0.033	0.033
29	0.018	0.018	0.018	0.018	-----	0.033	0.041	0.041	0.033	0.033	0.033	0.033
30	0.018	0.018	0.018	0.018	-----	0.033	0.051	0.041	0.033	0.033	0.033	0.033
31	0.018	-----	0.018	0.018	-----	0.033	-----	0.041	-----	0.033	0.033	-----
Maks.	0.041	0.025	0.033	0.025	0.018	0.041	0.051	0.090	0.041	0.033	0.033	0.033
Min.	0.018	0.018	0.018	0.018	0.018	0.018	0.033	0.041	0.033	0.033	0.033	0.033
Ortalama	0.025	0.023	0.018	0.018	0.018	0.026	0.035	0.045	0.034	0.033	0.033	0.033
LT/SN/Km2	8.10	7.38	5.86	5.86	5.86	8.51	11.4	14.5	11.0	10.7	10.7	10.7
AKIM mm.	21.7	19.1	15.7	15.7	14.2	22.8	29.5	38.9	28.5	28.8	28.8	27.9
MİL. M3	0.067	0.059	0.048	0.048	0.044	0.070	0.091	0.119	0.088	0.088	0.088	0.086

SU YILI (2006) YILLIK TOPLAM AKIM 0.90 MİLYON M3 292 MM. 9.2 LT/SN/Km2

15. Kizilirmak Havzasi

D15A302 ALKAYA DERESİ HAYRANLI

YERİ : **SİVAS MERKEZ HAYRANLI KÖYÜNDEDİR.**
36°5'59" Doğu - 39°47'36" Kuzey

YAĞIŞ ALANI : **3,94 km2** **YAKLAŞIK KOT : 1431 m**

GÖZLEM SÜRESİ : **01.10.2004 - 30.09.2006**

ORTALAMA AKIMLAR : **Gözlem süresinde 0.010 m3/sn. (2 Yıllık) 2006 Su yılında 0.009 m3/sn.**

ANLIK EN ÇOK VE EN AZ AKIMLAR:

2006 Su yılında anlık ençok akım	**:**	**0.125 m3/sn**	**05.05.2006**
2006 Su yılında anlık enaz akım	**:**	**0.001 m3/sn**	**06.02.2006**
Gözlem süresinde anlık ençok akım	**:**	**0.170 m3/sn**	**26.04.2005**
Gözlem süresinde anlık enaz akım	**:**	**0.001 m3/sn**	**06.02.2006**

Akımlar 01 Ekim 2005 'den 30 Eylül 2006' a kadar m3/sn olarak

Gün	Ekim	Kasım	Aralık	Ocak	Şubat	Mart	Nisan	Mayıs	Haziran	Temmuz	Ağustos	Eylül
01	0.004	0.004	0.004	0.004	0.004	0.004	0.014	0.068	0.008	0.008	0.002	0.004
02	0.004	0.004	0.004	0.002	0.004	0.008	0.014	0.068	0.008	0.008	0.002	0.004
03	0.004	0.004	0.004	0.002	0.004	0.008	0.022	0.068	0.008	0.008	0.002	0.004
04	0.004	0.004	0.004	0.002	0.004	0.008	0.014	0.054	0.008	0.008	0.002	0.004
05	0.004	0.004	0.004	0.002	0.002	0.008	0.014	0.082	0.008	0.008	0.002	0.004
06	0.004	0.004	0.004	0.004	0.002	0.008	0.014	0.068	0.008	0.008	0.002	0.004
07	0.004	0.004	0.002	0.004	0.002	0.008	0.014	0.054	0.008	0.008	0.002	0.004
08	0.004	0.004	0.002	0.004	0.004	0.008	0.014	0.082	0.008	0.008	0.002	0.004
09	0.004	0.004	0.002	0.004	0.004	0.008	0.014	0.068	0.008	0.008	0.002	0.004
10	0.004	0.004	0.002	0.004	0.004	0.008	0.014	0.068	0.008	0.008	0.002	0.004
11	0.004	0.004	0.002	0.004	0.004	0.008	0.014	0.054	0.008	0.008	0.004	0.004
12	0.004	0.004	0.002	0.004	0.004	0.008	0.014	0.022	0.008	0.008	0.004	0.004
13	0.004	0.004	0.002	0.004	0.004	0.008	0.008	0.008	0.008	0.008	0.004	0.004
14	0.004	0.004	0.002	0.004	0.004	0.004	0.008	0.008	0.008	0.004	0.004	0.004
15	0.004	0.004	0.002	0.004	0.004	0.004	0.022	0.008	0.008	0.004	0.004	0.004
16	0.004	0.004	0.004	0.004	0.004	0.004	0.043	0.008	0.008	0.004	0.004	0.004
17	0.004	0.004	0.004	0.004	0.004	0.004	0.043	0.014	0.008	0.004	0.004	0.004
18	0.004	0.004	0.004	0.004	0.004	0.008	0.054	0.008	0.008	0.004	0.004	0.004
19	0.008	0.004	0.004	0.004	0.004	0.008	0.043	0.008	0.008	0.004	0.004	0.004
20	0.008	0.004	0.004	0.004	0.004	0.008	0.043	0.008	0.008	0.004	0.004	0.004
21	0.008	0.004	0.004	0.004	0.004	0.008	0.032	0.008	0.008	0.004	0.004	0.004
22	0.008	0.004	0.004	0.004	0.004	0.008	0.032	0.008	0.008	0.004	0.004	0.004
23	0.008	0.004	0.004	0.004	0.004	0.008	0.043	0.008	0.008	0.004	0.004	0.004
24	0.008	0.004	0.004	0.004	0.004	0.008	0.068	0.008	0.008	0.004	0.004	0.004
25	0.008	0.004	0.004	0.004	0.004	0.022	0.082	0.008	0.008	0.004	0.004	0.004
26	0.008	0.004	0.004	0.004	0.004	0.022	0.054	0.008	0.008	0.004	0.004	0.004
27	0.008	0.004	0.004	0.004	0.004	0.014	0.054	0.008	0.008	0.002	0.004	0.004
28	0.004	0.004	0.004	0.004	0.004	0.014	0.043	0.008	0.008	0.002	0.004	0.004
29	0.004	0.004	0.004	0.004	-----	0.014	0.054	0.008	0.008	0.002	0.004	0.004
30	0.004	0.004	0.004	0.004	-----	0.014	0.082	0.008	0.008	0.002	0.004	0.004
31	0.004	-----	0.004	0.004	-----	0.014	-----	0.008	-----	0.002	0.004	-----
Maks.	0.008	0.004	0.008	0.004	0.004	0.032	0.097	0.125	0.008	0.008	0.004	0.004
Min.	0.004	0.002	0.002	0.002	0.001	0.004	0.008	0.008	0.008	0.002	0.002	0.004
Ortalama	0.005	0.004	0.003	0.004	0.004	0.009	0.033	0.029	0.008	0.005	0.003	0.004
LT/SN/Km2	1.31	1.02	0.868	0.950	0.961	2.34	8.32	7.48	2.03	1.36	0.851	1.02
AKIM mm.	3.51	2.63	2.32	2.54	2.32	6.27	21.6	20.0	5.26	3.64	2.28	2.63
MİL. M3	0.014	0.010	0.009	0.010	0.009	0.025	0.085	0.079	0.021	0.014	0.009	0.010

SU YILI (2006) YILLIK TOPLAM AKIM 0.30 MİLYON M3 75 MM. 2.4 LT/SN/Km2

15. Kizilirmak Havzasi

D15A303 KIŞLA DERESİ KUŞÇU

YERİ : **SİVAS-ZARA İLÇESİ KUŞÇU KÖYÜNDEDİR.**
37°14'16" Doğu - 39°56'23" Kuzey

YAĞIŞ ALANI : **34,50 km2** **YAKLAŞIK KOT : 1407 m**

GÖZLEM SÜRESİ : **01.10.2004 - 30.09.2006**

ORTALAMA AKIMLAR : **Gözlem süresinde 0.386 m3/sn. (2 Yıllık) 2006 Su yılında 0.452 m3/sn.**

ANLIK EN ÇOK VE EN AZ AKIMLAR:

2006 Su yılında anlık ençok akım	**:**	**6.78**	**m3/sn**	**25.03.2006**
2006 Su yılında anlık enaz akım	**:**	**0.016**	**m3/sn**	**20.01.2006**
Gözlem süresinde anlık ençok akım	**:**	**6.78**	**m3/sn**	**25.03.2006**
Gözlem süresinde anlık enaz akım	**:**	**0.001**	**m3/sn**	**01.10.2004**

Akımlar 01 Ekim 2005 'den 30 Eylül 2006' a kadar m3/sn olarak

Gün	Ekim	Kasım	Aralık	Ocak	Şubat	Mart	Nisan	Mayıs	Haziran	Temmuz	Ağustos	Eylül
01	0.066	0.118	0.118	0.135	0.118	0.460	2.71	1.14	0.460	0.255	0.101	0.049
02	0.049	0.135	0.118	0.135	0.101	0.578	2.62	1.31	0.460	0.225	0.083	0.049
03	0.066	0.135	0.118	0.135	0.118	0.814	2.08	1.31	0.637	0.225	0.083	0.083
04	0.083	0.135	0.118	0.118	0.118	0.932	1.82	1.14	0.696	0.195	0.066	0.083
05	0.066	0.165	0.118	0.118	0.101	0.873	1.99	1.31	0.696	0.195	0.066	0.049
06	0.066	0.135	0.101	0.135	0.135	1.05	1.99	1.39	0.460	0.195	0.066	0.083
07	0.066	0.135	0.101	0.135	0.135	1.65	1.99	1.82	0.390	0.195	0.066	0.066
08	0.066	0.118	0.101	0.135	0.135	2.71	2.35	1.73	0.390	0.195	0.049	0.066
09	0.066	0.118	0.101	0.118	0.165	2.26	2.80	1.48	0.355	0.165	0.049	0.036
10	0.066	0.118	0.101	0.118	0.135	1.48	2.53	1.31	0.390	0.165	0.049	0.036
11	0.066	0.118	0.101	0.118	0.165	1.14	2.17	1.14	0.355	0.135	0.049	0.036
12	0.049	0.118	0.101	0.118	0.195	1.05	1.99	1.05	0.320	0.135	0.049	0.049
13	0.066	0.118	0.083	0.118	0.195	1.22	1.99	0.991	0.355	0.135	0.049	0.066
14	0.066	0.101	0.083	0.118	0.195	1.56	1.82	0.932	0.355	0.118	0.049	0.049
15	0.066	0.101	0.101	0.083	0.165	1.99	1.73	0.932	0.355	0.118	0.049	0.066
16	0.118	0.118	0.118	0.066	0.118	1.56	1.65	0.873	0.320	0.118	0.049	0.066
17	0.165	0.118	0.118	0.066	0.165	1.39	1.39	0.932	0.320	0.118	0.036	0.066
18	0.118	0.101	0.118	0.083	0.195	1.22	1.22	0.814	0.255	0.118	0.036	0.049
19	0.195	0.118	0.195	0.101	0.195	1.14	1.14	0.814	0.255	0.135	0.036	0.049
20	0.135	0.135	0.195	0.066	0.195	0.991	1.05	0.755	0.255	0.135	0.036	0.036
21	0.118	0.165	0.165	0.049	0.195	0.932	0.991	0.696	0.255	0.135	0.066	0.049
22	0.118	0.195	0.135	0.101	0.195	0.991	0.932	0.696	0.255	0.118	0.049	0.066
23	0.101	0.165	0.135	0.101	0.195	1.22	0.932	0.637	0.255	0.118	0.049	0.066
24	0.101	0.135	0.135	0.101	0.225	1.73	0.991	0.637	0.285	0.118	0.049	0.083
25	0.083	0.135	0.118	0.118	0.255	4.12	1.14	0.578	0.285	0.118	0.036	0.083
26	0.101	0.135	0.118	0.118	0.320	2.71	0.932	0.578	0.255	0.118	0.049	0.101
27	0.083	0.135	0.101	0.101	0.355	2.08	0.932	0.637	0.255	0.135	0.049	0.101
28	0.083	0.135	0.066	0.083	0.355	2.08	0.873	0.578	0.255	0.118	0.049	0.083
29	0.101	0.118	0.083	0.101	-----	1.99	0.932	0.519	0.255	0.118	0.049	0.083
30	0.101	0.118	0.083	0.118	-----	2.17	1.39	0.519	0.255	0.118	0.049	0.083
31	0.118	-----	0.101	0.135	-----	2.35	-----	0.519	-----	0.101	0.036	-----
Maks.	0.285	0.225	0.225	0.460	0.519	6.78	4.36	2.26	0.755	0.255	0.118	0.118
Min.	0.036	0.101	0.026	0.016	0.036	0.425	0.814	0.225	0.225	0.083	0.020	0.016
Ortalama	0.091	0.130	0.114	0.108	0.184	1.56	1.64	0.960	0.356	0.148	0.053	0.064
LT/SN/Km2	2.63	3.76	3.32	3.13	5.32	45.3	47.4	27.8	10.3	4.29	1.54	1.86
AKIM mm.	7.04	9.75	8.89	8.38	12.9	121.	123.	74.5	26.8	11.5	4.12	4.83
MİL. M3	0.243	0.336	0.307	0.289	0.444	4.19	4.24	2.57	0.924	0.397	0.142	0.167

SU YILI (2006) YILLIK TOPLAM AKIM 14.25 MİLYON M3 413 MM. 13.1 LT/SN/Km2

15. Kizilirmak Havzasi

D15A304 GEVEN DERE KARATAŞ

YERİ : **SİVAS -ULAŞ İLÇESİ KARATAŞ KÖYÜ GİRİŞİNDEDİR.**
37°3'33" Doğu - 39°22'42" Kuzey

YAĞIŞ ALANI : **23,50 km2** **YAKLAŞIK KOT : 1438 m**

GÖZLEM SÜRESİ : **01.10.2004 - 30.09.2006**

ORTALAMA AKIMLAR : **Gözlem süresinde 0.020 m3/sn. (2 Yıllık) 2006 Su yılında 0.018 m3/sn.**

ANLIK EN ÇOK VE EN AZ AKIMLAR:

2006 Su yılında anlık ençok akım	**:**	**1.12**	**m3/sn**	**02.05.2006**
2006 Su yılında anlık enaz akım	**:**	**0.000**	**m3/sn**	**08.08.2006**
Gözlem süresinde anlık ençok akım	**:**	**1.73**	**m3/sn**	**16.07.2005**
Gözlem süresinde anlık enaz akım	**:**	**0.000**	**m3/sn**	**08.08.2006**

Akımlar 01 Ekim 2005 'den 30 Eylül 2006' a kadar m3/sn olarak

Gün	Ekim	Kasım	Aralık	Ocak	Şubat	Mart	Nisan	Mayıs	Haziran	Temmuz	Ağustos	Eylül
01	0.003	0.022	0.013	0.008	0.013	0.013	0.022	0.088	0.022	0.008	0.003	KURU
02	0.008	0.022	0.013	0.008	0.013	0.013	0.022	0.328	0.022	0.008	0.003	KURU
03	0.008	0.022	0.013	0.008	0.013	0.013	0.022	0.160	0.022	0.013	0.003	KURU
04	0.008	0.022	0.013	0.008	0.013	0.013	0.022	0.088	0.013	0.013	0.003	KURU
05	0.008	0.032	0.013	0.008	0.013	0.013	0.022	0.072	0.013	0.032	0.003	KURU
06	0.008	0.022	0.013	0.008	0.013	0.013	0.022	0.072	0.013	0.013	0.003	KURU
07	0.008	0.013	0.013	0.008	0.013	0.013	0.022	0.072	0.013	0.008	0.003	KURU
08	0.008	0.013	0.013	0.008	0.013	0.022	0.022	0.072	0.013	0.013	KURU	KURU
09	0.013	0.013	0.013	0.008	0.013	0.022	0.022	0.058	0.022	0.013	KURU	KURU
10	0.013	0.013	0.013	0.008	0.013	0.022	0.022	0.058	0.032	0.022	KURU	KURU
11	0.013	0.013	0.013	0.008	0.013	0.022	0.022	0.032	0.022	0.022	KURU	KURU
12	0.008	0.013	0.013	0.008	0.013	0.022	0.022	0.032	0.013	0.013	KURU	KURU
13	0.008	0.013	0.013	0.013	0.013	0.022	0.022	0.032	0.013	0.013	KURU	KURU
14	0.008	0.013	0.013	0.013	0.013	0.022	0.022	0.058	0.013	0.013	KURU	KURU
15	0.008	0.013	0.013	0.013	0.013	0.022	0.022	0.058	0.013	0.008	KURU	KURU
16	0.013	0.013	0.013	0.013	0.013	0.022	0.022	0.058	0.013	0.008	KURU	KURU
17	0.013	0.013	0.013	0.013	0.013	0.022	0.022	0.180	0.013	0.008	KURU	KURU
18	0.013	0.013	0.013	0.013	0.013	0.022	0.022	0.072	0.013	0.008	KURU	KURU
19	0.013	0.013	0.013	0.013	0.013	0.022	0.022	0.058	0.013	0.008	KURU	KURU
20	0.013	0.013	0.013	0.013	0.013	0.022	0.032	0.058	0.013	0.008	KURU	KURU
21	0.013	0.013	0.013	0.013	0.013	0.022	0.032	0.058	0.013	0.003	KURU	KURU
22	0.013	0.013	0.008	0.013	0.013	0.022	0.022	0.044	0.008	0.003	KURU	KURU
23	0.013	0.013	0.008	0.013	0.013	0.022	0.032	0.058	0.008	0.003	KURU	KURU
24	0.013	0.013	0.008	0.013	0.013	0.022	0.122	0.044	0.008	0.003	KURU	KURU
25	0.013	0.013	0.008	0.013	0.013	0.022	0.224	0.032	0.008	0.003	KURU	KURU
26	0.013	0.013	0.008	0.013	0.013	0.022	0.072	0.032	0.008	0.003	KURU	KURU
27	0.013	0.013	0.008	0.013	0.013	0.022	0.032	0.022	0.008	0.003	KURU	KURU
28	0.013	0.013	0.008	0.013	0.013	0.022	0.032	0.032	0.008	0.003	KURU	KURU
29	0.022	0.013	0.008	0.013	-----	0.022	0.044	0.032	0.022	0.003	KURU	KURU
30	0.022	0.013	0.008	0.013	-----	0.022	0.285	0.022	0.008	0.003	KURU	KURU
31	0.022	-----	0.008	0.013	-----	0.022	-----	0.022	-----	0.003	KURU	-----
Maks.	0.122	0.044	0.013	0.013	0.013	0.022	0.652	1.12	0.044	0.570	0.003	KURU
Min.	0.001	0.013	0.008	0.008	0.013	0.013	0.022	0.022	0.008	0.003	KURU	KURU
Ortalama	0.012	0.015	0.011	0.011	0.013	0.020	0.045	0.068	0.014	0.009	0.001	KURU
LT/SN/Km2	0.501	0.644	0.485	0.471	0.553	0.850	1.91	2.89	0.600	0.391	0.029	0.000
AKIM mm.	1.34	1.67	1.30	1.26	1.34	2.28	4.95	7.74	1.56	1.05	0.077	0.000
MİL. M3	0.032	0.039	0.030	0.030	0.031	0.053	0.116	0.182	0.037	0.025	0.002	0.000

SU YILI (2006) YILLIK TOPLAM AKIM 0.58 MİLYON M3 25 MM. 0.8 LT/SN/Km2

15. Kizilirmak Havzasi

D15A306 YILDIZ IRMAĞI ALİAĞILI

YERİ : **SİVAS MERKEZ GAZİBEY KÖYÜNÜN ALİAĞILI MEVKİNDEDİR**
36°51'55" Doğu - 39°59'44" Kuzey

YAĞIŞ ALANI : **660,00 km2** **YAKLAŞIK KOT : 1325 m**

GÖZLEM SÜRESİ : **01.10.2005 - 30.09.2006**

ORTALAMA AKIMLAR : **Gözlem süresinde 5.449 m3/sn. (1 Yıllık) 2006 Su yılında 5.449 m3/sn.**

ANLIK EN ÇOK VE EN AZ AKIMLAR:

2006 Su yılında anlık ençok akım	:	**75.2**	**m3/sn**	**25.03.2006**
2006 Su yılında anlık enaz akım	:	**0.608**	**m3/sn**	**18.09.2006**
Gözlem süresinde anlık ençok akım	:	**75.2**	**m3/sn**	**25.03.2006**
Gözlem süresinde anlık enaz akım	:	**0.608**	**m3/sn**	**18.09.2006**

Akımlar 01 Ekim 2005 'den 30 Eylül 2006' a kadar m3/sn olarak

Gün	Ekim	Kasım	Aralık	Ocak	Şubat	Mart	Nisan	Mayıs	Haziran	Temmuz	Ağustos	Eylül
01	1.37	1.55	2.30	1.93	1.68	16.9	19.3	10.1	4.64	2.43	1.93	1.55
02	1.37	1.68	2.18	1.93	2.05	21.1	26.4	11.2	4.20	2.43	1.80	1.46
03	1.37	1.68	2.05	1.93	1.93	23.8	29.1	12.4	4.06	2.30	1.68	1.55
04	1.37	1.80	1.93	1.93	1.80	35.8	23.8	10.1	3.78	2.30	1.68	1.55
05	1.37	1.80	1.93	2.05	1.80	22.6	20.8	10.9	3.64	2.43	1.55	1.46
06	1.37	1.68	1.93	2.18	2.05	26.0	18.1	11.2	3.64	2.55	1.55	1.37
07	1.37	1.80	1.93	2.30	2.18	29.8	16.9	9.77	3.50	2.80	1.37	1.28
08	1.37	1.80	1.93	2.43	2.68	47.3	16.6	13.0	3.08	2.30	1.46	1.28
09	1.28	1.80	1.80	2.30	2.94	41.1	17.5	11.5	3.08	2.05	1.46	1.19
10	1.19	1.80	1.80	2.18	2.68	25.1	19.0	10.4	2.94	2.05	1.37	1.28
11	1.19	1.68	1.80	2.18	3.08	17.2	20.5	9.19	2.94	2.05	1.37	1.28
12	1.19	1.55	1.80	2.18	4.86	14.2	17.8	8.40	2.94	2.05	1.37	1.28
13	1.19	1.55	1.68	2.18	5.08	13.0	14.5	8.15	2.68	2.18	1.46	1.19
14	1.28	1.68	1.80	2.18	4.06	14.2	13.0	8.65	2.80	2.30	1.37	1.28
15	1.46	1.68	1.93	2.05	3.92	16.0	12.4	7.40	2.80	2.30	1.46	1.28
16	1.68	1.55	2.18	1.93	3.36	13.6	14.5	7.15	2.68	2.18	1.46	1.37
17	1.68	1.68	2.18	1.80	3.22	13.6	11.8	14.8	2.68	2.05	1.55	1.19
18	1.68	1.80	2.05	1.80	3.50	13.6	10.1	14.8	2.55	2.05	1.55	1.10
19	1.80	1.80	2.18	2.18	3.22	14.2	8.90	12.1	2.43	2.18	1.46	1.10
20	1.80	1.80	1.93	1.93	2.94	12.7	8.65	9.77	2.30	2.30	1.68	1.19
21	1.68	1.80	1.93	1.68	2.94	11.8	8.15	8.65	2.30	2.30	1.55	1.37
22	1.55	1.55	1.93	1.80	2.94	13.3	7.65	7.90	2.18	2.18	1.37	1.46
23	1.55	1.46	1.93	1.93	2.94	14.2	7.40	7.15	2.30	2.30	1.37	1.55
24	1.55	1.37	1.93	1.80	3.08	16.0	7.90	6.40	2.18	2.30	1.46	1.37
25	1.68	1.80	1.93	2.05	3.36	39.9	8.40	5.74	2.18	2.18	1.46	1.37
26	1.55	1.93	1.80	1.93	4.42	62.9	7.90	5.52	2.05	2.05	1.55	1.46
27	1.55	2.05	1.80	1.80	7.40	42.9	7.15	7.65	2.18	2.05	1.55	1.46
28	1.80	2.18	1.55	1.46	9.48	31.2	6.90	8.65	2.18	2.05	1.46	1.46
29	1.68	2.30	1.68	1.55	-----	24.4	7.15	6.40	2.18	1.93	1.46	1.46
30	1.68	2.30	1.68	1.46	-----	21.1	9.19	5.52	2.30	1.93	1.37	1.46
31	1.68	-----	1.93	1.46	-----	20.8	-----	4.86	-----	1.80	1.37	-----
Maks.	2.05	2.68	2.55	2.55	16.0	75.2	30.2	19.0	5.52	2.94	2.43	2.18
Min.	1.01	0.920	1.10	0.740	1.01	10.9	5.96	3.92	1.68	1.46	0.920	0.608
Ortalama	1.49	1.76	1.92	1.95	3.41	23.6	13.9	9.21	2.85	2.20	1.50	1.36
LT/SN/Km2	2.26	2.67	2.90	2.96	5.17	35.7	21.1	14.0	4.31	3.34	2.28	2.05
AKIM mm.	6.07	6.93	7.78	7.92	12.5	95.6	54.6	37.4	11.2	8.95	6.09	5.32
MİL. M3	4.00	4.57	5.13	5.23	8.26	63.1	36.1	24.7	7.38	5.91	4.02	3.51

SU YILI (2006) YILLIK TOPLAM AKIM 171.91 MİLYON M3 260 MM. 8.3 LT/SN/Km2

15. Kizilirmak Havzasi

D15A308 AVCIÖZÜ DERESİ TAYYİP

YERİ : YOZGAT-HATTUSAŞYOLUNUN 10.KM SINDEKI KÖPRÜNÜN ALTINDADIR
34°42'1" Doğu - 39°50'18" Kuzey

YAĞIŞ ALANI : 53,00 km2 **YAKLAŞIK KOT :** 1118 m

GÖZLEM SÜRESİ : 01.10.2005 - 30.09.2006

ORTALAMA AKIMLAR : Gözlem süresinde 0.208 m3/sn. (1 Yıllık) 2006 Su yılında 0.208 m3/sn.

ANLIK EN ÇOK VE EN AZ AKIMLAR:

2006 Su yılında anlık ençok akım	:	3.02	m3/sn	01.03.2006
2006 Su yılında anlık enaz akım	:	0.000	m3/sn	01.10.2005
Gözlem süresinde anlık ençok akım	:	3.02	m3/sn	01.03.2006
Gözlem süresinde anlık enaz akım	:	0.000	m3/sn	01.10.2005

1. Anahtar Eğrisi (Seviyeler cm olarak)

Seviye	Akım	Seviye	Akım	Seviye	Akım	Seviye	Akım
1	0.000	10	0.130	31	1.9	52	5.0
3	0.000	11	0.173	36	2.4	61	5.6
5	0.004	16	0.395	41	3.2	71	6.5
7	0.038	21	0.786	46	4.0	81	7.4
9	0.082	26	1.3	51	4.8	86	7.8

Akımlar 01 Ekim 2005 'den 30 Eylül 2006' a kadar m3/sn olarak

Gün	Ekim	Kasım	Aralık	Ocak	Şubat	Mart	Nisan	Mayıs	Haziran	Temmuz	Ağustos	Eylül
01	KURU	KURU	0.173	0.082	0.082	1.98	0.473	0.351	0.057	0.010	KURU	KURU
02	KURU	KURU	0.173	0.082	0.082	1.50	0.473	0.708	0.057	0.010	KURU	KURU
03	KURU	KURU	0.173	0.082	0.082	1.86	0.395	0.630	0.057	0.010	KURU	KURU
04	KURU	0.002	0.173	0.082	0.082	1.26	0.351	0.630	0.057	0.010	KURU	KURU
05	KURU	0.002	0.173	0.082	0.082	0.976	0.306	0.551	0.038	0.004	KURU	KURU
06	KURU	0.004	0.173	0.173	0.082	0.881	0.306	0.395	0.038	0.004	KURU	KURU
07	KURU	0.010	0.173	0.217	0.262	0.708	0.306	0.351	0.038	0.004	KURU	KURU
08	KURU	0.038	0.173	0.217	0.551	0.786	0.262	0.351	0.038	0.004	KURU	KURU
09	KURU	0.057	0.173	0.173	0.708	0.786	0.262	0.351	0.057	0.004	KURU	KURU
10	KURU	0.082	0.173	0.130	0.708	0.630	0.262	0.306	0.130	0.004	KURU	KURU
11	KURU	0.082	0.173	0.130	1.07	0.630	0.262	0.306	0.173	0.004	KURU	KURU
12	KURU	0.082	0.082	0.130	1.26	0.551	0.262	0.306	0.173	0.004	KURU	KURU
13	KURU	0.082	0.082	0.130	0.708	0.551	0.217	0.217	0.130	0.004	KURU	KURU
14	KURU	0.082	0.082	0.082	0.473	0.551	0.217	0.173	0.173	0.004	KURU	KURU
15	KURU	0.082	0.082	0.082	0.351	0.473	0.306	0.173	0.173	0.004	KURU	KURU
16	KURU	0.082	0.082	0.082	0.351	0.473	0.395	0.130	0.173	0.004	KURU	KURU
17	KURU	0.082	0.130	0.082	0.306	0.473	0.306	0.130	0.173	0.002	KURU	KURU
18	KURU	0.082	0.130	0.082	0.306	0.473	0.262	0.130	0.173	0.002	KURU	KURU
19	KURU	0.082	0.130	0.082	0.630	0.551	0.262	0.082	0.173	0.002	KURU	KURU
20	KURU	0.082	0.082	0.082	0.708	1.26	0.217	0.082	0.173	0.002	KURU	KURU
21	KURU	0.082	0.082	0.130	0.976	1.62	0.217	0.082	0.130	KURU	KURU	KURU
22	KURU	0.082	0.082	0.082	1.07	1.50	0.351	0.082	0.082	KURU	KURU	KURU
23	KURU	0.082	0.082	0.038	1.17	1.17	0.351	0.082	0.082	KURU	KURU	KURU
24	KURU	0.082	0.082	0.038	1.38	0.881	0.351	0.082	0.082	KURU	KURU	KURU
25	KURU	0.082	0.082	0.038	1.62	0.881	0.306	0.057	0.130	KURU	KURU	KURU
26	KURU	0.082	0.082	0.038	1.74	1.07	0.262	0.057	0.082	KURU	KURU	KURU
27	KURU	0.082	0.082	0.038	1.74	0.976	0.262	0.057	0.130	KURU	KURU	KURU
28	KURU	0.082	0.082	0.038	1.38	0.786	0.306	0.057	0.038	KURU	KURU	KURU
29	KURU	0.082	0.082	0.057	-----	0.630	0.306	0.057	0.010	KURU	KURU	KURU
30	KURU	0.082	0.082	0.082	-----	0.551	0.351	0.057	0.010	KURU	KURU	KURU
31	KURU	-----	0.082	0.082	-----	0.551	-----	0.057	-----	KURU	KURU	-----
Maks.	KURU	0.082	0.173	0.262	2.73	3.02	2.33	1.17	0.217	0.010	KURU	KURU
Min.	KURU	KURU	0.038	0.038	0.082	0.473	0.173	0.057	0.010	KURU	KURU	KURU
Ortalama	KURU	0.061	0.119	0.095	0.713	0.902	0.306	0.228	0.101	0.003	KURU	KURU
LT/SN/Km2	0.000	1.15	2.24	1.79	13.5	17.0	5.76	4.31	1.91	0.058	0.000	0.000
AKIM mm.	0.000	2.99	6.01	4.80	32.5	45.6	14.9	11.5	4.94	0.156	0.000	0.000
MİL. M3	0.000	0.159	0.319	0.254	1.72	2.42	0.792	0.612	0.262	0.008	0.000	0.000

SU YILI (2006) YILLIK TOPLAM AKIM 6.55 MİLYON M3 124 MM. 3.9 LT/SN/Km2

16

KONYA KAPALI HAVZASI

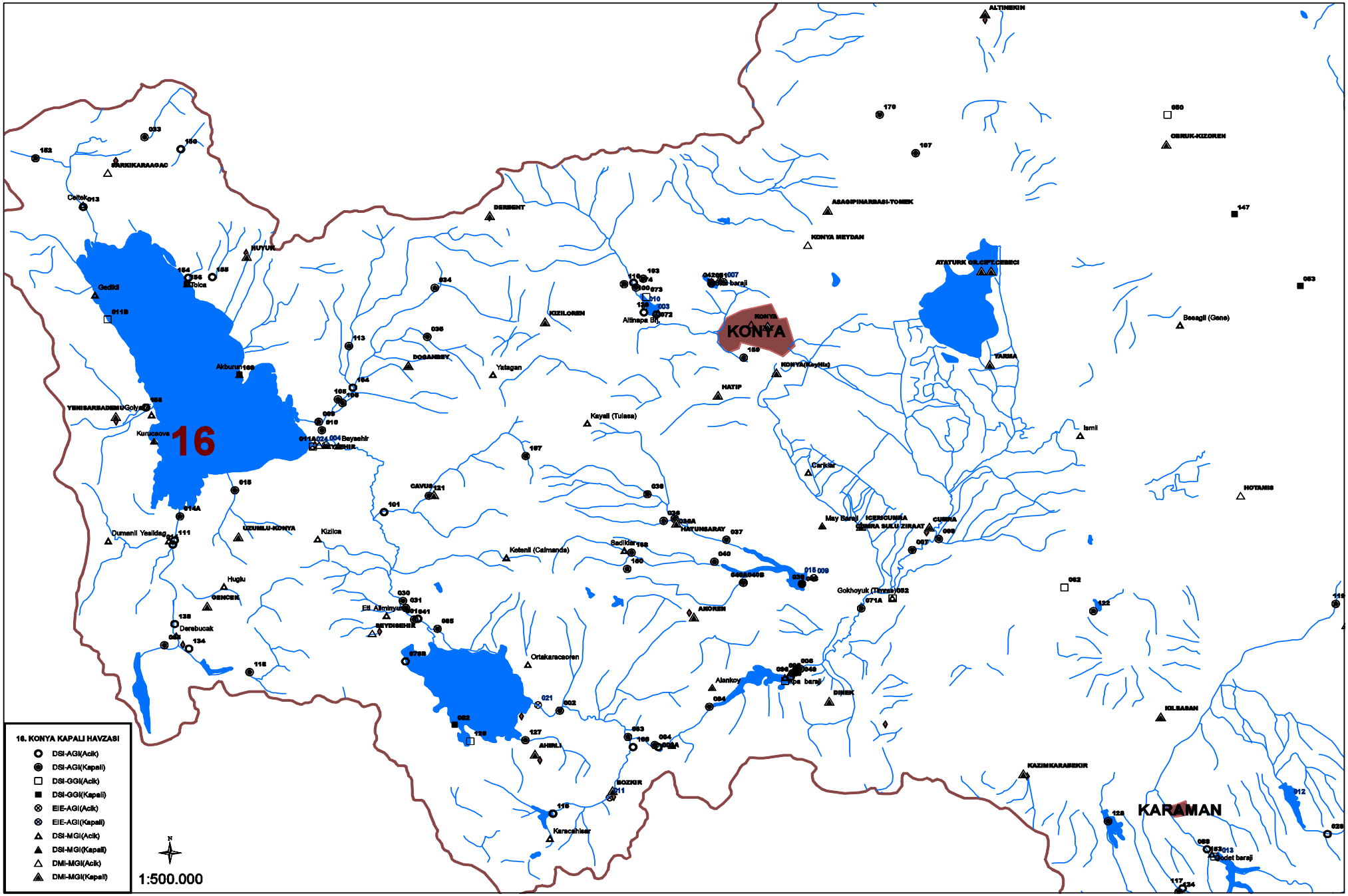
16
KONYA
KARAMAN
16. KONYA KAPALI HAVZASI
DSI-AGI(Acik)
DSI-AGI(Kapali)
DSI-GGI(Acik)
DSI-GGI(Kapali)
EIE-AGI(Acik)
EIE-AGI(Kapali)
DSI-MGI(Acik)
DSI-MGI(Kapali)
DMI-MGI(Acik)
DMI-MGI(Kapali)
1:500.000
N
ALTINEKIN
OBRUK-KIZOREN
ASAGIPINARBASI-TONEK
KONYA MEYDAN
ATATURK GR.CIFT.CERECI
DERBENT
HUYUK
Cetek
Gedikli
Tolca
Akburun
YENISARBADEM
Golyaka
Kurucaova
Beysehir
KIZILOREN
Altinapa Bir.
Besagil (Gene)
TARMA
DOGANBEY
Yatagan
KONYA(Kayalla)
HATIP
Kayali (Tulasa)
Ismil
Carikler
HOTAMIS
CAVUS
May Baraji
ICERSUMMA
CUMRA
UZUMLU-KONYA
Kizilca
Dumanli Yesildag
Ketenli (Calmanda)
Sadikler
HARUNSARAY
Huglu
DENCEK
Gokhoyuk (Tanca)
AKOREN
Etl. Alminyu
SEYDISEHIR
Derebucak
Ortakaracaoren
Alankoy
Apa baraji
DINEK
KILBABAN
AHIRLI
BOZKIR
KAZIMKARABEKIR
Karaahisar
Sodet baraji

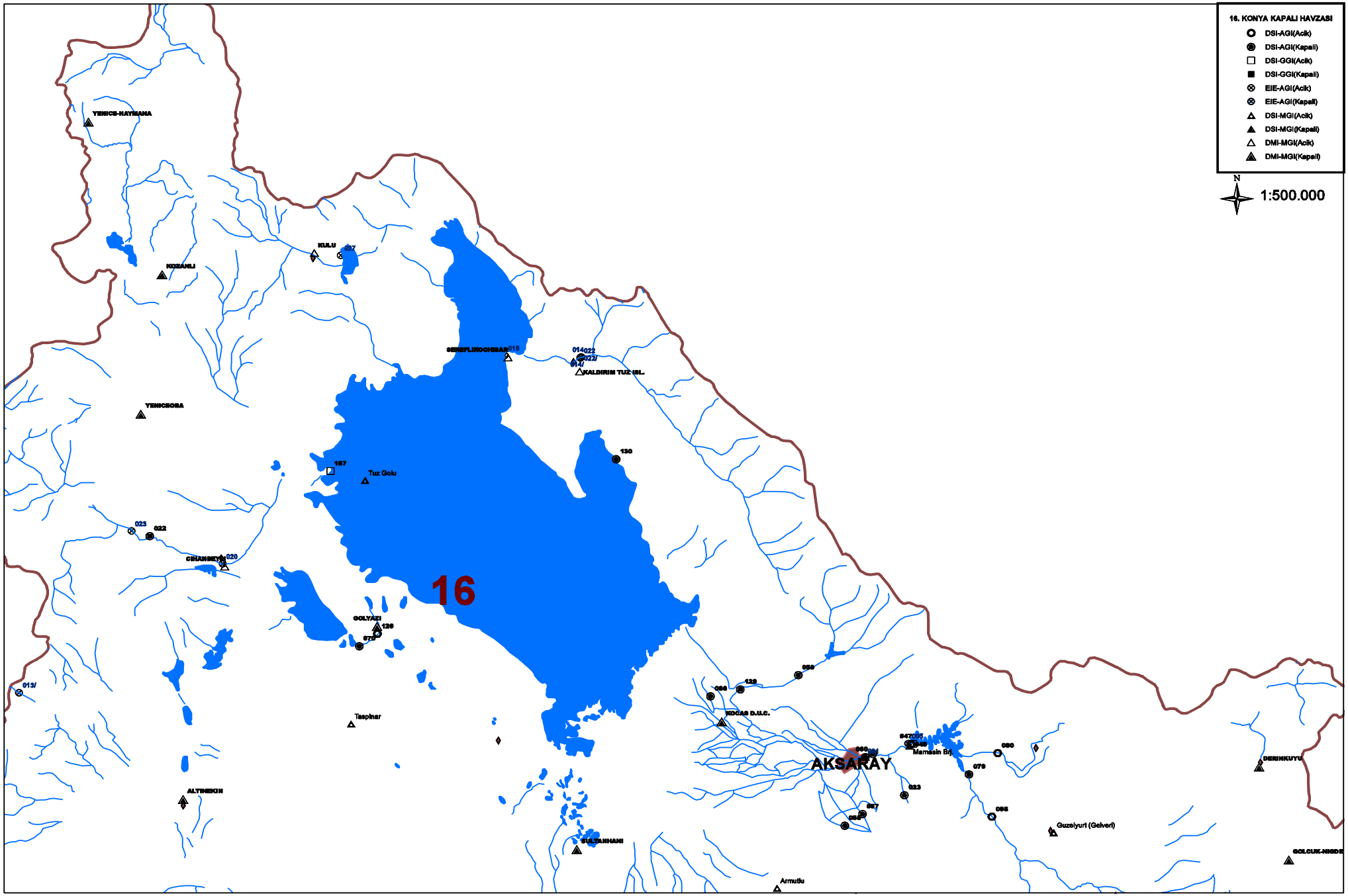
16. KONYA KAPALI HAVZASI
DSI-AGI(Acik)
DSI-AGI(Kapali)
DSI-GGI(Acik)
DSI-GGI(Kapali)
EIE-AGI(Acik)
EIE-AGI(Kapali)
DSI-MGI(Acik)
DSI-MGI(Kapali)
DMI-MGI(Acik)
DMI-MGI(Kapali)
N
1:500.000
16
AKSARAY
YENICE-HAYMANA
KOZANLI
KULU
SEREFLIKOCHISAR
KALDIRIM TUZ ISL.
YENICEOBA
Tuz Golu
CIHANBEYLI
GOLYAZI
Tasapinar
ALTINEKIN
SULTANHANI
Armutlu
KOCAS D.U.C.
Mamasin Brj.
Guzelyurt (Gelveri)
DERINKUYU
GOLCUK-NIGDE

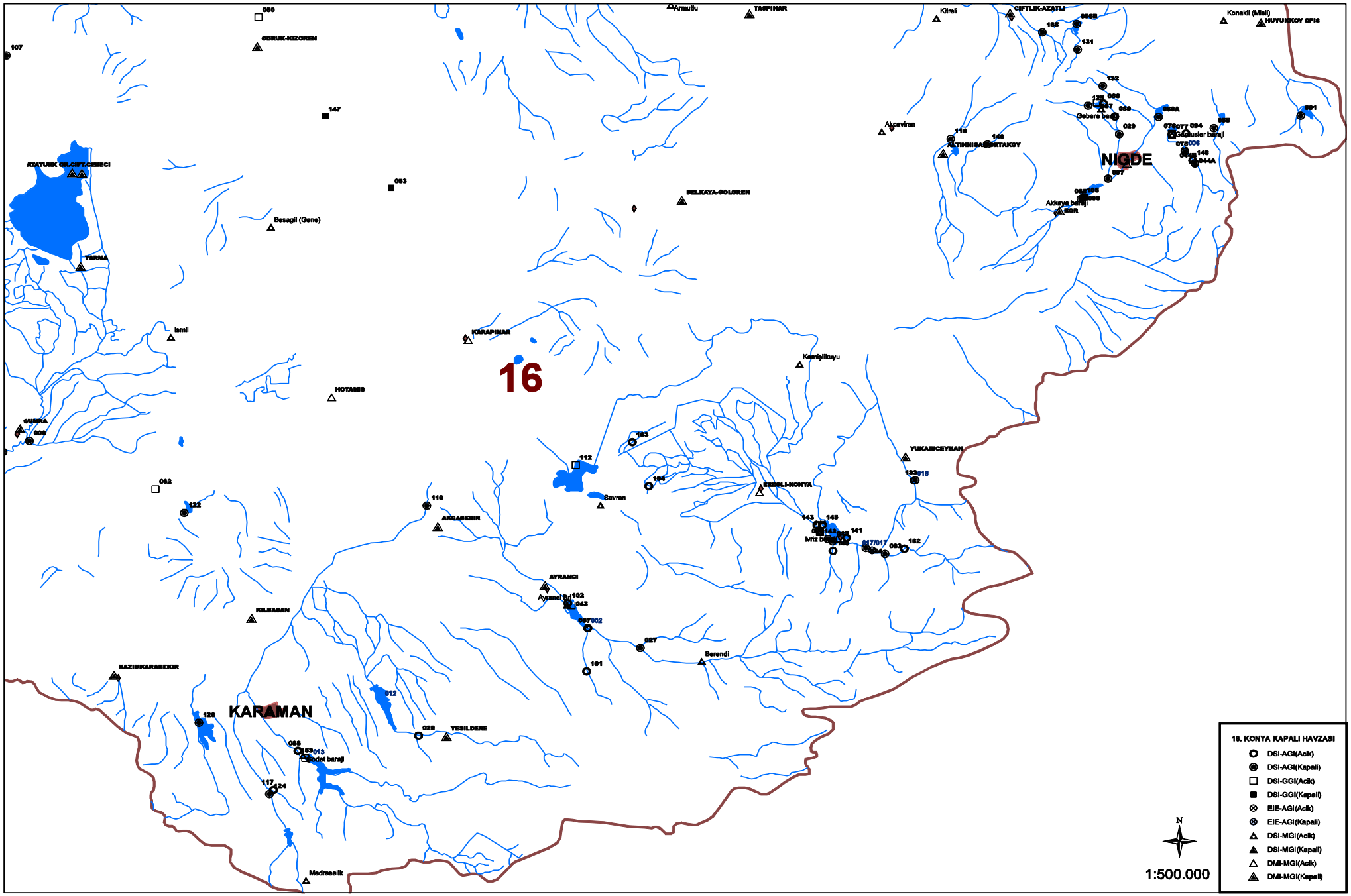
16
NIGDE
KARAMAN
Armutlu
TASPINAR
Kitreli
CIFTLIK-AZATLI
Konakli (Misli)
HUYUKKOY OPIS
OBRUK-KIZOREN
ATATURK GR.CIFT.CEBECI
Besagil (Gene)
YARMA
Ismil
KARAPINAR
HOTAMIS
CUMRA
SELKAYA-GOLOREN
Akcaviran
ALTINNISA-ORTAKOY
Gebere baraji
Akkaya baraji
Kamisilkuyu
YUKARICEYMAN
ERMELI-KONYA
Savran
AKCASEHIR
Ivriz baraji
AYRANCI
Ayranci Bd
KILBASAN
Berendi
KAZIMKARABEKIR
YESILDERE
Bodet baraji
Medreselik
N
1:500.000
16. KONYA KAPALI HAVZASI
DSI-AGI(Acik)
DSI-AGI(Kapali)
DSI-GGI(Acik)
DSI-GGI(Kapali)
EIE-AGI(Acik)
EIE-AGI(Kapali)
DSI-MGI(Acik)
DSI-MGI(Kapali)
DMI-MGI(Acik)
DMI-MGI(Kapali)

16. Konya Kapali Havzasi

D16A003 ÇARŞAMBA S. MAVİ

YERİ : **KONYA-ÇUMRA YOLUNDAN BOZKIR-HADİM YOLUNA GİRİLİR AKVİRAN İLÇESİNİ GEÇEREK AVDAN KÖYÜNDEN MAVİ BOĞAZINA VARILIR.**
32°19'33" Doğu - 37°15'34" Kuzey

YAĞIŞ ALANI : **64160,00 km2** **YAKLAŞIK KOT : 1060 m**

GÖZLEM SÜRESİ : **01.01.1959 - 30.09.2006**

ORTALAMA AKIMLAR : **Gözlem süresinde 13.683 m3/sn. (57 Yıllık) 2006 Su yılında 10.148 m3/sn.**

ANLIK EN ÇOK VE EN AZ AKIMLAR:

2006 Su yılında anlık ençok akım	:	**58.7**	**m3/sn**	**16.04.2006**
2006 Su yılında anlık enaz akım	:	**0.000**	**m3/sn**	**31.10.2005**
Gözlem süresinde anlık ençok akım	:	**100.**	**m3/sn**	**20.03.1951**
Gözlem süresinde anlık enaz akım	:	**0.000**	**m3/sn**	**08.12.1999**

Akımlar 01 Ekim 2005 'den 30 Eylül 2006' a kadar m3/sn olarak

Gün	Ekim	Kasım	Aralık	Ocak	Şubat	Mart	Nisan	Mayıs	Haziran	Temmuz	Ağustos	Eylül
01	KURU	KURU	0.464	0.230	1.20	25.5	30.5	41.0	3.90	7.60	0.699	0.464
02	KURU	KURU	0.347	0.230	1.20	22.5	31.0	40.5	3.90	5.40	0.464	0.581
03	KURU	KURU	0.347	0.230	1.20	21.5	30.0	41.0	3.70	3.70	0.347	0.464
04	KURU	KURU	0.464	0.230	1.05	24.0	29.0	42.0	7.20	3.10	0.347	0.347
05	KURU	KURU	0.347	0.230	1.05	23.5	33.0	42.0	4.10	2.80	0.347	0.230
06	KURU	KURU	0.230	0.230	1.05	22.5	36.5	42.5	3.40	2.52	0.347	0.080
07	KURU	KURU	0.581	0.230	1.80	22.0	50.3	41.5	3.90	3.90	0.464	KURU
08	KURU	KURU	0.581	0.347	2.70	21.5	51.0	37.0	3.90	1.20	0.464	KURU
09	KURU	KURU	0.230	0.464	3.70	22.0	51.7	13.0	2.16	0.816	0.464	KURU
10	KURU	KURU	0.080	0.464	3.10	21.0	51.0	11.8	1.35	0.581	0.464	KURU
11	KURU	KURU	0.080	0.464	3.40	20.0	50.3	13.4	1.65	1.20	0.464	KURU
12	KURU	KURU	KURU	0.464	6.60	19.5	49.6	16.2	1.35	3.10	0.464	KURU
13	KURU	KURU	KURU	0.464	23.5	20.5	48.9	13.4	27.0	3.40	0.699	KURU
14	KURU	KURU	KURU	0.581	16.6	27.5	46.8	12.6	27.5	3.40	0.816	KURU
15	KURU	KURU	KURU	0.581	12.6	19.0	46.1	10.5	28.0	3.70	0.464	KURU
16	KURU	KURU	KURU	0.581	13.0	18.2	54.5	9.40	28.5	4.40	0.581	KURU
17	KURU	KURU	KURU	0.581	13.4	21.0	53.1	11.8	28.5	4.60	0.581	KURU
18	KURU	KURU	KURU	0.581	12.6	27.0	51.0	12.2	28.0	4.60	0.464	KURU
19	KURU	KURU	0.155	0.581	13.0	28.0	49.6	12.2	28.0	4.60	0.464	KURU
20	KURU	0.230	0.581	1.80	14.2	28.0	47.5	12.6	27.5	7.60	0.464	KURU
21	KURU	0.933	0.581	1.50	17.4	27.5	42.5	10.3	28.5	7.20	0.464	KURU
22	KURU	0.933	0.464	1.20	20.0	27.0	44.7	7.60	30.0	3.70	0.464	KURU
23	KURU	0.581	0.464	1.20	20.0	28.0	44.0	5.20	26.5	2.80	0.464	KURU
24	KURU	0.464	0.464	1.35	20.0	31.0	44.0	10.5	27.5	4.80	0.464	KURU
25	KURU	0.347	0.464	1.35	11.0	32.0	48.9	8.00	27.5	27.5	0.464	KURU
26	KURU	0.230	0.464	1.35	18.2	30.5	47.5	5.20	27.5	23.5	0.464	KURU
27	KURU	0.155	0.347	1.35	22.0	30.0	46.1	4.40	27.0	27.5	0.347	KURU
28	KURU	0.230	0.347	1.20	22.0	29.0	44.7	7.20	10.8	21.0	0.347	KURU
29	KURU	0.155	0.347	1.20	-----	29.5	44.7	6.40	5.20	3.90	0.347	KURU
30	KURU	0.230	0.347	1.05	-----	29.5	42.5	4.60	11.0	2.34	0.347	KURU
31	KURU	-----	0.230	1.20	-----	30.0	-----	4.10	-----	1.65	0.347	-----
Maks.	KURU	1.05	0.933	2.34	25.0	36.5	58.7	43.5	39.0	29.0	1.50	1.05
Min.	KURU	KURU	KURU	0.230	1.05	15.4	28.0	3.10	0.933	0.464	0.347	KURU
Ortalama	KURU	0.150	0.291	0.758	10.6	25.1	44.7	17.7	16.2	6.39	0.464	0.072
LT/SN/Km2	0.000	0.002	0.005	0.012	0.166	0.392	0.697	0.277	0.252	0.100	0.007	0.001
AKIM mm.	0.000	0.006	0.012	0.032	0.401	1.05	1.81	0.741	0.653	0.267	0.019	0.003
MİL. M3	0.000	0.388	0.778	2.03	25.7	67.3	116.	47.5	41.9	17.1	1.24	0.187

SU YILI (2006) YILLIK TOPLAM AKIM 320.12 MİLYON M3 5 MM. 0.2 LT/SN/Km2

16. Konya Kapali Havzasi

D16A013 ŞARKIKARAAGAÇ S. ÇELTEK KÖP.

YERİ : **Ş.KARAAĞAÇ -PINARŞAH-FAKILAR KÖYÜ YOLUNUN 12 KM SİNDEKİ ÇELTEK KÖYÜ CİVARINDADIR**

31°18'56" Doğu - 38°0'49" Kuzey

YAĞIŞ ALANI : **519,00 km2** **YAKLAŞIK KOT : 1145 m**

GÖZLEM SÜRESİ : **01.10.1960 - 30.09.2006**

ORTALAMA AKIMLAR : **Gözlem süresinde 1.037 m3/sn. (44 Yıllık) 2006 Su yılında 0.377 m3/sn.**

ANLIK EN ÇOK VE EN AZ AKIMLAR:

2006 Su yılında anlık ençok akım	**:**	**3.57**	**m3/sn**	**24.04.2006**
2006 Su yılında anlık enaz akım	**:**	**0.000**	**m3/sn**	**12.07.2006**
Gözlem süresinde anlık ençok akım	**:**	**41.0**	**m3/sn**	**30.01.1999**
Gözlem süresinde anlık enaz akım	**:**	**0.000**	**m3/sn**	**21.08.1990**

5. Anahtar Eğrisi (Seviyeler cm olarak)

Seviye	Akım	Seviye	Akım	Seviye	Akım	Seviye	Akım
1	0.000	11	0.066	41	2.4	141	23.0
3	0.000	13	0.110	61	5.4	161	29.5
5	0.000	15	0.170	81	9.8	181	36.0
7	0.016	21	0.420	101	14.0	191	39.0
9	0.035	31	1.2	121	18.0	201	41.0

Akımlar 01 Ekim 2005 'den 30 Eylül 2006' a kadar m3/sn olarak

Gün	Ekim	Kasım	Aralık	Ocak	Şubat	Mart	Nisan	Mayıs	Haziran	Temmuz	Ağustos	Eylül
01	0.110	0.110	0.110	0.110	0.035	0.376	1.30	0.800	0.244	0.420	0.170	0.420
02	0.110	0.110	0.110	0.110	0.066	0.376	1.30	0.960	0.200	0.420	0.170	0.376
03	0.110	0.110	0.110	0.110	0.066	0.376	1.30	1.04	0.200	0.332	0.170	0.332
04	0.110	0.110	0.110	0.110	0.066	0.376	1.20	0.960	0.200	0.332	0.170	0.496
05	0.110	0.110	0.110	0.110	0.086	0.288	1.20	0.960	0.200	0.244	0.170	0.572
06	0.110	0.110	0.110	0.110	0.086	0.288	1.12	0.960	0.200	0.200	0.170	0.496
07	0.110	0.140	0.110	0.110	0.110	0.288	1.04	0.960	0.572	0.200	0.170	0.648
08	0.110	0.140	0.110	0.110	0.110	0.288	1.04	0.880	0.244	0.170	0.170	0.496
09	0.110	0.170	0.110	0.110	0.110	0.288	0.960	0.724	0.332	0.110	0.170	0.376
10	0.140	0.170	0.110	0.110	0.110	0.496	0.724	0.724	0.332	0.066	0.170	0.288
11	0.140	0.200	0.110	0.110	0.170	0.496	0.648	0.724	0.332	0.066	0.170	0.200
12	0.170	0.200	0.110	0.110	0.170	0.376	1.04	0.572	0.332	KURU	0.170	0.420
13	0.140	0.200	0.110	0.110	0.170	0.332	0.572	0.496	0.332	KURU	0.170	0.496
14	0.140	0.244	0.110	0.110	0.170	0.724	0.420	0.420	0.376	KURU	0.170	0.880
15	0.140	0.244	0.110	0.110	0.200	1.84	0.420	0.420	0.376	KURU	0.170	0.496
16	0.140	0.244	0.110	0.110	0.244	3.31	0.420	0.420	0.376	KURU	0.170	0.376
17	0.110	0.244	0.110	0.035	0.244	3.18	0.420	0.420	0.376	KURU	0.200	0.332
18	0.110	0.200	0.110	0.035	0.332	3.18	0.376	0.496	0.376	KURU	0.200	0.332
19	0.110	0.200	0.110	0.035	0.332	2.66	0.332	0.420	0.332	KURU	0.200	0.332
20	0.110	0.170	0.140	0.035	0.376	3.05	0.332	0.420	0.332	KURU	0.200	0.244
21	0.110	0.170	0.140	0.035	0.376	2.53	0.332	0.376	0.332	KURU	0.200	0.170
22	0.110	0.140	0.140	0.035	0.376	2.12	0.332	0.376	0.332	KURU	0.200	0.170
23	0.110	0.140	0.140	0.035	0.376	1.70	0.376	0.332	0.288	KURU	0.200	0.140
24	0.110	0.110	0.140	0.035	0.376	1.60	3.57	0.288	0.288	KURU	0.200	0.140
25	0.110	0.110	0.110	0.035	0.420	1.70	2.79	0.288	0.376	KURU	0.170	0.140
26	0.110	0.110	0.110	0.035	0.420	1.84	1.84	0.288	0.376	KURU	0.170	0.140
27	0.110	0.110	0.110	0.035	0.420	1.84	1.40	0.288	0.376	KURU	0.170	0.140
28	0.110	0.110	0.110	0.035	0.420	1.84	1.20	0.244	0.420	KURU	0.170	0.140
29	0.110	0.110	0.110	0.035	-----	1.40	1.12	0.244	0.420	KURU	0.170	0.140
30	0.110	0.110	0.110	0.035	-----	1.40	0.960	0.244	0.420	KURU	0.200	0.140
31	0.110	-----	0.110	0.035	-----	1.40	-----	0.244	-----	KURU	0.200	-----
Maks.	0.170	0.244	0.140	0.140	0.420	3.31	3.57	1.04	0.572	0.420	0.200	0.880
Min.	0.110	0.110	0.110	0.035	0.035	0.288	0.332	0.244	0.200	KURU	0.170	0.140
Ortalama	0.118	0.155	0.115	0.074	0.230	1.35	1.00	0.548	0.330	0.083	0.180	0.336
LT/SN/Km2	0.227	0.298	0.221	0.142	0.443	2.61	1.93	1.06	0.635	0.159	0.346	0.647
AKIM mm.	0.608	0.773	0.593	0.380	1.07	6.98	5.01	2.83	1.65	0.426	0.927	1.68
MİL. M3	0.315	0.401	0.308	0.197	0.556	3.63	2.60	1.47	0.855	0.221	0.481	0.870

SU YILI (2006) YILLIK TOPLAM AKIM 11.90 MİLYON M3 23 MM. 0.7 LT/SN/Km2

16. Konya Kapali Havzasi

D16A014 Soguksu Yesildag

YERİ : **BEYŞEHİR-YEŞILDAĞ BELDESİ**
31°29'45" Doğu - 37°32'23" Kuzey

YAĞIŞ ALANI : **368,00 km2** **YAKLAŞIK KOT : 1113 m**

GÖZLEM SÜRESİ : **01.10.1991 - 30.09.2006**

ORTALAMA AKIMLAR : **Gözlem süresinde 2.943 m3/sn. (24 Yıllık) 2006 Su yılında 1.752 m3/sn.**

ANLIK EN ÇOK VE EN AZ AKIMLAR:

2006 Su yılında anlık ençok akım	**:**	**11.3**	**m3/sn**	**12.02.2006**
2006 Su yılında anlık enaz akım	**:**	**0.035**	**m3/sn**	**07.11.2005**
Gözlem süresinde anlık ençok akım	**:**	**37.0**	**m3/sn**	**07.06.1971**
Gözlem süresinde anlık enaz akım	**:**	**0.000**	**m3/sn**	**31.10.1991**

İstasyon için kullanılmış anahtar bulunamadı.

Akımlar 01 Ekim 2005 'den 30 Eylül 2006' a kadar m3/sn olarak

Gün	Ekim	Kasım	Aralık	Ocak	Şubat	Mart	Nisan	Mayıs	Haziran	Temmuz	Ağustos	Eylül
01	0.175	0.072	0.175	0.390	0.760	4.50	3.48	3.26	1.61	1.66	1.38	0.820
02	0.175	0.072	0.175	0.390	0.760	4.26	3.37	3.26	1.61	1.66	1.33	0.932
03	0.175	0.072	0.175	0.390	0.760	4.26	3.15	3.37	1.61	1.61	1.29	0.932
04	0.120	0.072	0.120	0.390	0.760	4.26	3.15	3.37	1.61	1.52	1.29	0.932
05	0.120	0.072	0.120	0.390	0.760	3.78	3.15	3.48	1.61	1.66	1.29	0.820
06	0.120	0.072	0.120	0.390	0.960	3.37	3.15	3.48	1.66	1.76	1.24	0.820
07	0.120	0.072	0.120	0.390	2.55	3.15	3.26	3.48	1.66	1.76	1.20	0.726
08	0.120	0.035	0.120	0.560	3.86	3.94	3.26	3.59	1.71	1.76	1.15	0.631
09	0.120	0.035	0.120	0.560	2.95	4.58	3.26	3.59	1.71	1.76	1.15	0.631
10	0.120	0.035	0.120	0.560	3.26	3.70	3.15	3.59	1.71	1.71	1.11	0.631
11	0.120	0.035	0.120	0.560	9.34	3.48	3.15	3.59	1.71	1.71	1.06	0.631
12	0.120	0.035	0.120	0.560	11.2	3.48	3.15	3.59	1.76	1.71	1.06	0.538
13	0.120	0.035	0.120	0.560	9.91	4.58	3.15	3.70	1.76	1.71	1.02	0.538
14	0.120	0.035	0.120	0.560	6.82	9.26	3.15	3.70	1.80	1.71	0.970	0.538
15	0.120	0.035	0.120	0.560	4.82	8.69	3.26	3.70	1.76	1.66	0.926	0.538
16	0.120	0.035	0.120	0.560	3.70	7.11	3.37	3.78	1.76	1.66	0.926	0.538
17	0.120	0.035	0.120	0.470	3.05	6.42	3.37	3.78	1.76	1.66	0.882	0.460
18	0.120	0.035	0.175	0.470	3.05	5.94	3.26	3.86	1.76	1.66	0.882	0.538
19	0.120	0.035	0.860	0.470	3.37	5.86	3.26	3.86	1.76	1.61	0.882	0.538
20	0.120	0.035	1.18	0.470	3.48	4.98	3.15	3.86	1.76	1.61	0.838	0.460
21	0.120	0.072	0.860	0.470	4.02	4.50	3.15	3.94	1.76	1.61	0.794	0.460
22	0.072	0.390	0.660	0.470	4.10	4.18	3.15	3.94	1.76	1.56	0.750	0.460
23	0.072	0.310	0.660	0.560	4.02	4.02	3.26	3.94	1.76	1.61	0.750	0.460
24	0.072	0.310	0.560	0.660	4.02	3.94	3.48	4.02	1.76	1.56	0.704	0.460
25	0.072	0.310	0.560	0.660	4.66	5.14	3.48	4.02	1.76	1.56	0.704	0.383
26	0.072	0.250	0.470	0.560	4.82	4.42	3.26	1.66	1.76	1.56	0.658	0.383
27	0.072	0.250	0.470	0.560	6.26	4.02	3.26	1.66	1.80	1.52	0.612	0.383
28	0.072	0.250	0.470	0.560	5.22	3.86	3.26	1.61	1.76	1.52	0.612	0.383
29	0.072	0.250	0.390	0.660	-----	3.70	3.26	1.56	1.76	1.52	0.566	0.383
30	0.072	0.250	0.470	0.660	-----	3.59	3.26	1.56	1.80	1.47	0.566	0.383
31	0.072	-----	0.390	0.660	-----	3.59	-----	1.56	-----	1.42	1.27	-----
Maks.	0.175	0.560	1.39	0.660	11.3	10.6	3.86	4.02	1.85	1.90	1.42	1.38
Min.	0.072	0.035	0.120	0.390	0.760	3.05	3.15	1.56	1.56	1.38	1.04	0.383
Ortalama	0.110	0.120	0.335	0.520	4.04	4.66	3.25	3.27	1.73	1.63	0.963	0.578
LT/SN/Km2	0.298	0.326	0.910	1.41	11.0	12.7	8.83	8.88	4.69	4.42	2.62	1.57
AKIM mm.	0.799	0.845	2.44	3.79	26.6	33.9	22.9	23.8	12.2	11.8	7.01	4.07
MİL. M3	0.294	0.311	0.897	1.39	9.78	12.5	8.42	8.76	4.47	4.36	2.58	1.50

SU YILI (2006) YILLIK TOPLAM AKIM 55.26 MİLYON M3 150 MM. 4.8 LT/SN/Km2

16. Konya Kapali Havzasi

D16A015 Üstünler S. Üstünler

YERİ : **BEYŞEHİR-ÜSTÜNLER YOLU ÜZERI.**
31°35'29" Doğu - 37°36'57" Kuzey

YAĞIŞ ALANI : **153,80 km2** **YAKLAŞIK KOT : 1126 m**

GÖZLEM SÜRESİ : **01.10.1991 - 30.09.2006**

ORTALAMA AKIMLAR : **Gözlem süresinde 1.485 m3/sn. (35 Yıllık) 2006 Su yılında 1.244 m3/sn.**

ANLIK EN ÇOK VE EN AZ AKIMLAR:

2006 Su yılında anlık ençok akım	**:**	**25.4**	**m3/sn**	**14.03.2006**
2006 Su yılında anlık enaz akım	**:**	**0.000**	**m3/sn**	**01.10.2005**
Gözlem süresinde anlık ençok akım	**:**	**51.9**	**m3/sn**	**07.02.2003**
Gözlem süresinde anlık enaz akım	**:**	**0.000**	**m3/sn**	**29.09.1973**

İstasyon için kullanılmış anahtar bulunamadı.

Akımlar 01 Ekim 2005 'den 30 Eylül 2006' a kadar m3/sn olarak

Gün	Ekim	Kasım	Aralık	Ocak	Şubat	Mart	Nisan	Mayıs	Haziran	Temmuz	Ağustos	Eylül
01	KURU	0.001	0.062	0.324	0.444	3.34	3.85	2.60	1.11	0.636	0.115	0.042
02	KURU	0.001	0.072	0.324	0.444	2.98	3.85	2.70	1.11	0.570	0.094	0.042
03	KURU	0.003	0.072	0.324	0.444	2.98	3.70	2.60	1.18	0.570	0.094	0.042
04	KURU	0.037	0.072	0.324	0.444	2.98	3.70	2.50	1.11	0.570	0.072	0.032
05	KURU	0.061	0.072	0.324	0.444	2.80	3.85	2.50	1.11	0.528	0.072	0.032
06	KURU	0.097	0.072	0.324	0.528	2.80	3.85	2.50	1.11	0.570	0.072	0.032
07	KURU	0.097	0.094	0.360	1.18	2.80	3.85	2.50	1.11	0.768	0.062	0.032
08	KURU	0.097	0.094	0.402	2.50	3.34	3.70	2.40	1.04	0.768	0.062	0.022
09	KURU	0.076	0.094	0.444	2.30	3.70	3.70	2.40	1.04	0.768	0.062	0.022
10	KURU	0.061	0.094	0.402	2.50	3.16	3.70	2.40	1.04	0.768	0.062	0.032
11	KURU	0.061	0.094	0.402	13.1	3.16	3.70	2.40	1.04	0.768	0.062	0.042
12	KURU	0.048	0.094	0.402	11.8	2.98	3.70	2.40	1.04	0.768	0.062	0.032
13	KURU	0.048	0.094	0.402	5.20	4.30	3.70	2.30	0.970	0.768	0.062	0.022
14	KURU	0.048	0.094	0.402	2.98	12.5	3.70	2.04	1.04	0.768	0.052	0.022
15	KURU	0.037	0.094	0.402	2.30	9.75	3.70	2.04	1.04	0.768	0.052	0.022
16	0.001	0.028	0.094	0.402	1.91	6.04	3.70	1.91	1.04	0.768	0.052	0.022
17	0.006	0.028	0.094	0.402	1.57	5.20	3.52	1.78	1.04	0.900	0.052	0.032
18	KURU	0.037	0.137	0.402	1.91	5.20	3.16	1.78	0.970	0.900	0.052	0.032
19	0.001	0.061	0.444	3.34	2.17	5.05	2.98	1.78	0.970	0.900	0.052	0.022
20	0.001	0.061	0.444	2.80	2.17	4.45	2.98	1.65	0.900	0.900	0.052	0.012
21	0.001	0.158	0.324	2.17	2.40	4.30	2.98	1.57	0.900	0.900	0.042	0.002
22	0.001	0.072	0.288	1.33	2.40	4.15	2.98	1.49	0.834	0.900	0.042	0.002
23	0.001	0.062	0.288	0.768	2.40	4.00	2.98	1.49	0.834	0.900	0.042	0.012
24	0.001	0.062	0.288	0.486	2.40	4.00	2.98	1.49	0.834	0.402	0.032	0.016
25	0.001	0.052	0.288	0.444	2.50	4.75	2.98	1.41	0.768	0.216	0.032	0.016
26	0.001	0.052	0.288	0.444	2.60	4.30	2.80	1.41	0.768	0.216	0.032	0.016
27	0.001	0.052	0.288	0.444	4.60	4.15	2.80	1.33	0.768	0.180	0.032	0.016
28	0.001	0.062	0.288	0.444	3.70	4.15	2.80	1.33	0.702	0.158	0.032	0.016
29	0.001	0.062	0.324	0.444	-----	4.00	2.70	1.25	0.636	0.115	0.022	0.016
30	0.001	0.062	0.324	0.444	-----	3.85	2.70	1.18	0.636	0.115	0.032	0.016
31	0.001	-----	0.324	0.444	-----	3.85	-----	1.04	-----	0.115	0.032	-----
Maks.	0.028	0.324	0.900	6.25	24.5	25.4	4.15	3.16	1.41	0.970	0.158	0.062
Min.	KURU	0.001	0.062	0.324	0.444	2.80	2.70	1.04	0.636	0.062	0.022	KURU
Ortalama	0.001	0.056	0.187	0.670	2.83	4.36	3.38	1.94	0.956	0.611	0.054	0.024
LT/SN/Km2	0.004	0.365	1.22	4.36	18.4	28.3	22.0	12.6	6.22	3.97	0.354	0.156
AKIM mm.	0.011	0.946	3.25	11.7	44.6	75.8	56.9	33.8	16.1	10.6	0.949	0.403
MİL. M3	0.002	0.145	0.501	1.79	6.85	11.7	8.75	5.20	2.48	1.64	0.146	0.062

SU YILI (2006) YILLIK TOPLAM AKIM 39.27 MİLYON M3 255 MM. 8.1 LT/SN/Km2

16. Konya Kapali Havzasi

D16A028 Ibrala Ç. Nalama Çiftligi

YERİ : **ISTASYON KARAMANDAN 29.7KM.MESAFEDE IBRALA NAHİYESI HUDUTLARI ICERISINDE NALAMA CIFTLIGINE TESIS EDILMISTIR.**
33°28'10" Doğu - 37°9'5" Kuzey

YAĞIŞ ALANI : **209,60 km2** **YAKLAŞIK KOT : 1125 m**

GÖZLEM SÜRESİ : **01.05.1958 - 30.09.2006**

ORTALAMA AKIMLAR : **Gözlem süresinde 1.816 m3/sn. (46 Yıllık) 2006 Su yılında 0.275 m3/sn.**

ANLIK EN ÇOK VE EN AZ AKIMLAR:

2006 Su yılında anlık ençok akım	**:**	**2.49**	**m3/sn**	**31.03.2006**
2006 Su yılında anlık enaz akım	**:**	**0.000**	**m3/sn**	**12.09.2006**
Gözlem süresinde anlık ençok akım	**:**	**145.**	**m3/sn**	**19.04.1984**
Gözlem süresinde anlık enaz akım	**:**	**0.000**	**m3/sn**	**01.11.1996**

İstasyon için kullanılmış anahtar bulunamadı.

Akımlar 01 Ekim 2005 'den 30 Eylül 2006' a kadar m3/sn olarak

Gün	Ekim	Kasım	Aralık	Ocak	Şubat	Mart	Nisan	Mayıs	Haziran	Temmuz	Ağustos	Eylül
01	0.023	0.045	0.108	0.108	0.149	1.70	1.70	0.396	0.149	0.073	0.045	0.001
02	0.023	0.045	0.108	0.149	0.149	1.22	1.94	0.396	0.108	0.073	0.023	0.001
03	0.023	0.073	0.108	0.149	0.149	1.11	1.94	0.303	0.108	0.073	0.023	0.001
04	0.023	0.108	0.108	0.149	0.149	1.11	1.57	0.303	0.108	0.073	0.023	0.001
05	0.023	0.108	0.108	0.149	0.108	1.11	1.22	0.303	0.108	0.073	0.023	0.001
06	0.023	0.108	0.108	0.108	0.108	1.11	1.11	0.258	0.073	0.108	0.023	0.001
07	0.010	0.149	0.073	0.073	0.149	0.993	0.881	0.258	0.073	0.108	0.010	0.001
08	0.010	0.073	0.073	0.073	0.258	1.22	0.993	0.303	0.073	0.108	0.010	0.001
09	0.010	0.073	0.073	0.073	0.396	1.11	0.993	0.303	0.108	0.108	0.023	0.001
10	0.010	0.045	0.073	0.073	0.396	0.993	1.22	0.303	0.108	0.108	0.023	0.001
11	0.010	0.045	0.073	0.073	0.303	0.769	1.22	0.303	0.108	0.073	0.023	0.001
12	0.010	0.045	0.073	0.073	0.489	0.881	0.993	0.258	0.108	0.073	0.023	KURU
13	0.010	0.045	0.073	0.073	0.676	0.881	0.993	0.258	0.108	0.073	0.023	KURU
14	0.010	0.045	0.073	0.073	0.676	0.769	0.993	0.258	0.108	0.073	0.023	KURU
15	0.010	0.045	0.073	0.073	0.676	0.769	0.881	0.258	0.108	0.073	0.023	KURU
16	0.010	0.045	0.073	0.073	0.583	0.769	0.993	0.258	0.108	0.073	0.023	KURU
17	0.023	0.045	0.073	0.073	0.583	0.881	1.33	0.258	0.108	0.073	0.023	KURU
18	0.023	0.045	0.073	0.073	0.583	0.881	0.993	0.258	0.108	0.073	0.023	KURU
19	0.045	0.045	0.108	0.073	0.489	0.881	0.769	0.258	0.073	0.073	0.023	KURU
20	0.073	0.045	0.108	0.073	0.396	0.881	0.676	0.258	0.073	0.073	0.010	KURU
21	0.023	0.045	0.108	0.073	0.489	0.881	0.489	0.258	0.073	0.073	0.010	KURU
22	0.010	0.045	0.108	0.073	0.489	0.993	0.396	0.258	0.073	0.073	0.010	KURU
23	0.010	0.073	0.108	0.073	0.489	0.993	0.396	0.258	0.073	0.073	0.010	KURU
24	0.010	0.108	0.108	0.073	0.583	1.82	0.396	0.258	0.073	0.073	0.010	KURU
25	0.010	0.108	0.108	0.108	0.993	2.12	0.396	0.258	0.073	0.073	0.010	KURU
26	0.010	0.108	0.108	0.206	1.33	1.57	0.396	0.206	0.073	0.073	0.010	KURU
27	0.010	0.108	0.108	0.149	1.70	1.22	0.396	0.149	0.073	0.073	0.001	KURU
28	0.010	0.108	0.108	0.149	1.82	1.22	0.396	0.149	0.073	0.073	0.001	KURU
29	0.010	0.108	0.108	0.149	-----	1.22	0.396	0.149	0.073	0.073	0.001	KURU
30	0.023	0.108	0.108	0.149	-----	1.22	0.396	0.149	0.073	0.045	0.001	KURU
31	0.023	-----	0.108	0.149	-----	1.82	-----	0.149	-----	0.045	0.001	-----
Maks.	0.073	0.303	0.149	0.206	1.94	2.49	2.30	0.396	0.149	0.108	0.045	0.001
Min.	0.010	0.023	0.073	0.073	0.108	0.769	0.396	0.108	0.045	0.045	0.001	KURU
Ortalama	0.018	0.073	0.094	0.103	0.549	1.13	0.915	0.258	0.092	0.077	0.016	0.000
LT/SN/Km2	0.085	0.349	0.451	0.490	2.62	5.40	4.37	1.23	0.438	0.367	0.078	0.002
AKIM mm.	0.227	0.905	1.21	1.31	6.33	14.5	11.3	3.29	1.14	0.982	0.209	0.005
MİL. M3	0.048	0.190	0.253	0.275	1.33	3.03	2.37	0.691	0.238	0.206	0.044	0.001

SU YILI (2006) YILLIK TOPLAM AKIM 8.68 MİLYON M3 41 MM. 1.3 LT/SN/Km2

16. Konya Kapali Havzasi

D16A048 Mamasin Brj. Çikis

YERİ : **AKSARAY MAMASIN BARAJI MANSABINDADIR.**
34°7'44" Doğu - 38°24'4" Kuzey

YAĞIŞ ALANI : **1383,00 km2** **YAKLAŞIK KOT : 1071 m**

GÖZLEM SÜRESİ : **20.02.1963 - 30.09.2006**

ORTALAMA AKIMLAR : **Gözlem süresinde 4.163 m3/sn. (39 Yıllık) 2006 Su yılında 2.185 m3/sn.**

ANLIK EN ÇOK VE EN AZ AKIMLAR:

2006 Su yılında anlık ençok akım	**:**	**15.4**	**m3/sn**	**10.06.2006**
2006 Su yılında anlık enaz akım	**:**	**0.000**	**m3/sn**	**01.10.2005**
Gözlem süresinde anlık ençok akım	**:**	**26.0**	**m3/sn**	**14.05.1967**
Gözlem süresinde anlık enaz akım	**:**	**0.000**	**m3/sn**	**06.06.1963**

İstasyon için kullanılmış anahtar bulunamadı.

Akımlar 01 Ekim 2005 'den 30 Eylül 2006' a kadar m3/sn olarak

Gün	Ekim	Kasım	Aralık	Ocak	Şubat	Mart	Nisan	Mayıs	Haziran	Temmuz	Ağustos	Eylül
01	KURU	KURU	KURU	KURU	KURU	KURU	KURU	14.3	14.6	KURU	0.880	KURU
02	KURU	KURU	KURU	KURU	KURU	KURU	KURU	14.3	14.6	0.026	0.026	KURU
03	KURU	KURU	KURU	KURU	KURU	KURU	KURU	14.3	14.6	2.04	KURU	KURU
04	KURU	KURU	KURU	KURU	KURU	KURU	KURU	14.3	15.0	2.38	KURU	KURU
05	KURU	KURU	KURU	KURU	KURU	KURU	KURU	14.3	15.0	0.610	KURU	KURU
06	KURU	KURU	KURU	KURU	KURU	KURU	KURU	14.3	15.0	KURU	KURU	KURU
07	KURU	KURU	KURU	KURU	KURU	KURU	KURU	14.3	15.0	KURU	KURU	KURU
08	KURU	KURU	KURU	KURU	KURU	KURU	KURU	14.3	15.0	KURU	KURU	KURU
09	KURU	KURU	KURU	KURU	KURU	KURU	KURU	13.2	15.4	KURU	KURU	KURU
10	KURU	KURU	KURU	KURU	KURU	KURU	KURU	12.0	15.4	KURU	0.050	KURU
11	KURU	KURU	KURU	KURU	KURU	KURU	KURU	12.0	15.0	KURU	2.92	KURU
12	KURU	KURU	KURU	KURU	KURU	KURU	KURU	12.0	15.0	KURU	0.050	KURU
13	KURU	KURU	KURU	KURU	KURU	KURU	KURU	12.0	14.6	KURU	KURU	KURU
14	KURU	KURU	KURU	KURU	KURU	KURU	KURU	11.7	14.3	KURU	KURU	KURU
15	KURU	KURU	KURU	KURU	KURU	KURU	KURU	11.3	14.3	KURU	KURU	KURU
16	KURU	KURU	KURU	KURU	KURU	KURU	KURU	10.7	13.9	KURU	KURU	KURU
17	KURU	KURU	KURU	KURU	KURU	KURU	0.080	8.20	13.9	0.026	KURU	KURU
18	KURU	KURU	KURU	KURU	KURU	KURU	6.31	0.160	13.9	1.01	KURU	KURU
19	KURU	KURU	KURU	KURU	KURU	KURU	11.0	1.56	13.5	0.400	KURU	KURU
20	KURU	KURU	KURU	KURU	KURU	KURU	11.3	1.56	13.5	KURU	KURU	KURU
21	KURU	KURU	KURU	KURU	KURU	KURU	11.3	2.04	13.2	KURU	KURU	KURU
22	KURU	KURU	KURU	KURU	KURU	KURU	11.3	9.13	11.0	KURU	KURU	KURU
23	KURU	KURU	KURU	KURU	KURU	KURU	11.7	7.93	0.120	KURU	KURU	KURU
24	KURU	KURU	KURU	KURU	KURU	KURU	13.5	7.39	KURU	KURU	KURU	KURU
25	KURU	KURU	KURU	KURU	KURU	KURU	13.9	7.39	KURU	KURU	KURU	KURU
26	KURU	KURU	KURU	KURU	KURU	KURU	13.9	7.39	KURU	KURU	KURU	KURU
27	KURU	KURU	KURU	KURU	KURU	KURU	13.9	7.39	KURU	KURU	KURU	KURU
28	KURU	KURU	KURU	KURU	KURU	KURU	14.3	7.39	KURU	KURU	KURU	KURU
29	KURU	KURU	KURU	KURU	-----	KURU	14.3	8.82	KURU	KURU	KURU	KURU
30	KURU	KURU	KURU	KURU	-----	KURU	14.3	10.4	KURU	KURU	KURU	KURU
31	KURU	-----	KURU	KURU	-----	KURU	-----	14.3	-----	0.026	KURU	-----
Maks.	KURU	KURU	KURU	KURU	KURU	KURU	14.3	14.6	15.4	2.38	4.20	KURU
Min.	KURU	KURU	KURU	KURU	KURU	KURU	KURU	KURU	KURU	KURU	KURU	KURU
Ortalama	KURU	KURU	KURU	KURU	KURU	KURU	5.37	10.0	10.5	0.210	0.127	KURU
LT/SN/Km2	0.000	0.000	0.000	0.000	0.000	0.000	3.88	7.24	7.61	0.152	0.092	0.000
AKIM mm.	0.000	0.000	0.000	0.000	0.000	0.000	10.1	19.4	19.7	0.407	0.245	0.000
MİL. M3	0.000	0.000	0.000	0.000	0.000	0.000	13.9	26.8	27.3	0.563	0.339	0.000

SU YILI (2006) YILLIK TOPLAM AKIM 68.90 MİLYON M3 50 MM. 1.6 LT/SN/Km2

16. Konya Kapali Havzasi

D16A066 Gebere Brj. Çikis

YERİ : **NİĞDE-MERKEZ.**
34°38'19" Doğu - 38°2'50" Kuzey

YAĞIŞ ALANI : **17,40 km2** **YAKLAŞIK KOT : 1696 m**

GÖZLEM SÜRESİ : **20.09.1964 - 30.09.2006**

ORTALAMA AKIMLAR : **Gözlem süresinde 0.061 m3/sn. (34 Yıllık) 2006 Su yılında 0.067 m3/sn.**

ANLIK EN ÇOK VE EN AZ AKIMLAR:

2006 Su yılında anlık ençok akım	**:**	**0.280 m3/sn**	**15.08.2006**
2006 Su yılında anlık enaz akım	**:**	**0.000 m3/sn**	**01.10.2005**
Gözlem süresinde anlık ençok akım	**:**	**0.620 m3/sn**	**10.08.1976**
Gözlem süresinde anlık enaz akım	**:**	**0.000 m3/sn**	**01.10.1969**

İstasyon için kullanılmış anahtar bulunamadı.

Akımlar 01 Ekim 2005 'den 30 Eylül 2006' a kadar m3/sn olarak

Gün	Ekim	Kasım	Aralık	Ocak	Şubat	Mart	Nisan	Mayıs	Haziran	Temmuz	Ağustos	Eylül
01	KURU	KURU	KURU	KURU	KURU	KURU	KURU	KURU	0.033	0.190	0.210	0.210
02	KURU	KURU	KURU	KURU	KURU	KURU	KURU	KURU	0.170	0.210	0.230	0.210
03	KURU	KURU	KURU	KURU	KURU	KURU	KURU	KURU	0.170	0.260	0.230	0.210
04	KURU	KURU	KURU	KURU	KURU	KURU	KURU	KURU	0.170	0.260	0.230	0.210
05	KURU	KURU	KURU	KURU	KURU	KURU	KURU	KURU	0.170	0.210	0.230	0.210
06	KURU	KURU	KURU	KURU	KURU	KURU	KURU	KURU	0.170	0.210	0.230	0.190
07	KURU	KURU	KURU	KURU	KURU	KURU	KURU	KURU	0.170	0.210	0.260	0.190
08	KURU	KURU	KURU	KURU	KURU	KURU	KURU	KURU	0.170	0.210	0.260	0.190
09	KURU	KURU	KURU	KURU	KURU	KURU	KURU	KURU	0.170	0.210	0.260	0.190
10	KURU	KURU	KURU	KURU	KURU	KURU	KURU	KURU	0.170	0.210	0.260	0.190
11	KURU	KURU	KURU	KURU	KURU	KURU	KURU	KURU	0.170	0.210	0.230	0.190
12	KURU	KURU	KURU	KURU	KURU	KURU	KURU	KURU	0.170	0.230	0.230	0.190
13	KURU	KURU	KURU	KURU	KURU	KURU	KURU	KURU	0.170	0.230	0.230	0.190
14	KURU	KURU	KURU	KURU	KURU	KURU	KURU	KURU	0.170	0.230	0.260	0.190
15	KURU	KURU	KURU	KURU	KURU	KURU	KURU	KURU	0.190	0.230	0.280	0.190
16	KURU	KURU	KURU	KURU	KURU	KURU	KURU	KURU	0.190	0.230	0.280	0.190
17	KURU	KURU	KURU	KURU	KURU	KURU	KURU	KURU	0.210	0.230	0.280	0.190
18	KURU	KURU	KURU	KURU	KURU	KURU	KURU	KURU	0.210	0.230	0.280	0.170
19	KURU	KURU	KURU	KURU	KURU	KURU	KURU	KURU	0.210	0.230	0.260	0.170
20	KURU	KURU	KURU	KURU	KURU	KURU	KURU	KURU	0.210	0.230	0.260	0.170
21	KURU	KURU	KURU	KURU	KURU	KURU	KURU	KURU	0.210	0.230	0.260	0.170
22	KURU	KURU	KURU	KURU	KURU	KURU	KURU	KURU	0.210	0.230	0.230	0.170
23	KURU	KURU	KURU	KURU	KURU	KURU	KURU	KURU	0.210	0.230	0.230	0.130
24	KURU	KURU	KURU	KURU	KURU	KURU	KURU	KURU	0.210	0.210	0.230	0.075
25	KURU	KURU	KURU	KURU	KURU	KURU	KURU	KURU	0.210	0.230	0.230	KURU
26	KURU	KURU	KURU	KURU	KURU	KURU	KURU	KURU	0.210	0.230	0.260	KURU
27	KURU	KURU	KURU	KURU	KURU	KURU	KURU	KURU	0.210	0.230	0.260	KURU
28	KURU	KURU	KURU	KURU	KURU	KURU	KURU	KURU	0.210	0.260	0.230	KURU
29	KURU	KURU	KURU	KURU	-----	KURU	KURU	KURU	0.210	0.260	0.230	KURU
30	KURU	KURU	KURU	KURU	-----	KURU	KURU	KURU	0.210	0.260	0.230	KURU
31	KURU	-----	KURU	KURU	-----	KURU	-----	KURU	-----	0.230	0.230	-----
Maks.	KURU	KURU	KURU	KURU	KURU	KURU	KURU	KURU	0.210	0.260	0.280	0.230
Min.	KURU	KURU	KURU	KURU	KURU	KURU	KURU	KURU	KURU	0.190	0.210	KURU
Ortalama	KURU	KURU	KURU	KURU	KURU	KURU	KURU	KURU	0.185	0.228	0.245	0.146
LT/SN/Km2	0.000	0.000	0.000	0.000	0.000	0.000	0.000	0.000	10.7	13.1	14.1	8.40
AKIM mm.	0.000	0.000	0.000	0.000	0.000	0.000	0.000	0.000	27.6	35.1	37.8	21.8
MİL. M3	0.000	0.000	0.000	0.000	0.000	0.000	0.000	0.000	0.481	0.610	0.658	0.379

SU YILI (2006) YILLIK TOPLAM AKIM 2.13 MİLYON M3 122 MM. 3.9 LT/SN/Km2

16. Konya Kapali Havzasi

D16A072 Altinapa Brj. Çikis

YERİ : **KONYA-KIRŞEHİR YOLUNUN 20. KM SINDEKI ALTINAPA BARAJININ ÇIKIŞINDADIR.**
32°18'29" Doğu - 37°52'49" Kuzey

YAĞIŞ ALANI : **566,20 km2** **YAKLAŞIK KOT : 1223 m**

GÖZLEM SÜRESİ : **14.12.1966 - 30.09.2006**

ORTALAMA AKIMLAR : **Gözlem süresinde 1.340 m3/sn. (28 Yıllık) 2006 Su yılında 0.152 m3/sn.**

ANLIK EN ÇOK VE EN AZ AKIMLAR:

2006 Su yılında anlık ençok akım	**:**	**4.44**	**m3/sn**	**07.06.2006**
2006 Su yılında anlık enaz akım	**:**	**0.000**	**m3/sn**	**01.10.2005**
Gözlem süresinde anlık ençok akım	**:**	**33.0**	**m3/sn**	**14.05.1967**
Gözlem süresinde anlık enaz akım	**:**	**0.000**	**m3/sn**	**10.11.1967**

İstasyon için kullanılmış anahtar bulunamadı.

Akımlar 01 Ekim 2005 'den 30 Eylül 2006' a kadar m3/sn olarak

Gün	Ekim	Kasım	Aralık	Ocak	Şubat	Mart	Nisan	Mayıs	Haziran	Temmuz	Ağustos	Eylül
01	KURU	KURU	KURU	KURU	KURU	KURU	KURU	KURU	KURU	KURU	KURU	KURU
02	KURU	KURU	KURU	KURU	KURU	KURU	KURU	KURU	KURU	KURU	KURU	KURU
03	KURU	KURU	KURU	KURU	KURU	KURU	KURU	KURU	KURU	KURU	KURU	KURU
04	KURU	KURU	KURU	KURU	KURU	KURU	KURU	KURU	0.442	KURU	KURU	KURU
05	KURU	KURU	KURU	KURU	KURU	KURU	KURU	KURU	3.41	KURU	KURU	KURU
06	KURU	KURU	KURU	KURU	KURU	KURU	KURU	KURU	4.34	KURU	KURU	KURU
07	KURU	KURU	KURU	KURU	KURU	KURU	KURU	KURU	4.44	KURU	KURU	KURU
08	KURU	KURU	KURU	KURU	KURU	KURU	KURU	KURU	4.02	KURU	KURU	KURU
09	KURU	KURU	KURU	KURU	KURU	KURU	KURU	KURU	2.75	KURU	KURU	KURU
10	KURU	KURU	KURU	KURU	KURU	KURU	KURU	KURU	2.29	KURU	KURU	KURU
11	KURU	KURU	KURU	KURU	KURU	KURU	KURU	KURU	0.798	KURU	KURU	KURU
12	KURU	KURU	KURU	KURU	KURU	KURU	KURU	KURU	0.020	KURU	KURU	KURU
13	KURU	KURU	KURU	KURU	KURU	KURU	KURU	KURU	KURU	0.499	KURU	KURU
14	KURU	KURU	KURU	KURU	KURU	KURU	KURU	KURU	KURU	3.71	KURU	KURU
15	KURU	KURU	KURU	KURU	KURU	KURU	KURU	KURU	KURU	3.92	KURU	KURU
16	KURU	KURU	KURU	KURU	KURU	KURU	KURU	KURU	KURU	3.03	KURU	KURU
17	KURU	KURU	KURU	KURU	KURU	KURU	KURU	KURU	KURU	1.29	KURU	KURU
18	KURU	KURU	KURU	KURU	KURU	KURU	KURU	KURU	KURU	1.14	KURU	KURU
19	KURU	KURU	KURU	KURU	KURU	KURU	KURU	KURU	KURU	0.798	KURU	KURU
20	KURU	KURU	KURU	KURU	KURU	KURU	KURU	KURU	KURU	0.020	0.337	KURU
21	KURU	KURU	KURU	KURU	KURU	KURU	KURU	KURU	KURU	KURU	2.65	KURU
22	KURU	KURU	KURU	KURU	KURU	KURU	KURU	KURU	KURU	KURU	3.03	KURU
23	KURU	KURU	KURU	KURU	KURU	KURU	KURU	KURU	KURU	KURU	3.60	KURU
24	KURU	KURU	KURU	KURU	KURU	KURU	KURU	KURU	KURU	KURU	3.60	KURU
25	KURU	KURU	KURU	KURU	KURU	KURU	KURU	KURU	KURU	KURU	3.41	KURU
26	KURU	KURU	KURU	KURU	KURU	KURU	KURU	KURU	KURU	KURU	1.94	KURU
27	KURU	KURU	KURU	KURU	KURU	KURU	KURU	KURU	KURU	KURU	0.047	KURU
28	KURU	KURU	KURU	KURU	KURU	KURU	KURU	KURU	KURU	KURU	KURU	KURU
29	KURU	KURU	KURU	KURU	-----	KURU	KURU	KURU	KURU	KURU	KURU	KURU
30	KURU	KURU	KURU	KURU	-----	KURU	KURU	KURU	KURU	KURU	KURU	KURU
31	KURU	-----	KURU	KURU	-----	KURU	-----	KURU	-----	KURU	KURU	-----
Maks.	KURU	KURU	KURU	KURU	KURU	KURU	KURU	KURU	4.44	4.02	3.60	KURU
Min.	KURU	KURU	KURU	KURU	KURU	KURU	KURU	KURU	KURU	KURU	KURU	KURU
Ortalama	KURU	KURU	KURU	KURU	KURU	KURU	KURU	KURU	0.750	0.465	0.600	KURU
LT/SN/Km2	0.000	0.000	0.000	0.000	0.000	0.000	0.000	0.000	1.33	0.821	1.06	0.000
AKIM mm.	0.000	0.000	0.000	0.000	0.000	0.000	0.000	0.000	3.43	2.20	2.84	0.000
MİL. M3	0.000	0.000	0.000	0.000	0.000	0.000	0.000	0.000	1.94	1.24	1.61	0.000

SU YILI (2006) YILLIK TOPLAM AKIM 4.79 MİLYON M3 8 MM. 0.3 LT/SN/Km2

16. Konya Kapali Havzasi

D16A077 Gümüsler Brj. Çikis

YERİ : **NİĞDE/GÜMÜŞLER BELDESİ.**
34°45'40" Doğu - 38°0'31" Kuzey

YAĞIŞ ALANI : **69,20 km2** **YAKLAŞIK KOT : 1330 m**

GÖZLEM SÜRESİ : **09.08.1967 - 30.09.2006**

ORTALAMA AKIMLAR : **Gözlem süresinde 0.107 m3/sn. (32 Yıllık) 2006 Su yılında 0.077 m3/sn.**

ANLIK EN ÇOK VE EN AZ AKIMLAR:

2006 Su yılında anlık encok akım	:	**0.468**	**m3/sn**	**07.09.2006**
2006 Su yılında anlık enaz akım	:	**0.000**	**m3/sn**	**03.10.2005**
Gözlem süresinde anlık encok akım	:	**55.0**	**m3/sn**	**14.08.1979**
Gözlem süresinde anlık enaz akım	:	**0.000**	**m3/sn**	**01.10.1968**

İstasyon için kullanılmış anahtar bulunamadı.

Akımlar 01 Ekim 2005 'den 30 Eylül 2006' a kadar m3/sn olarak

Gün	Ekim	Kasım	Aralık	Ocak	Şubat	Mart	Nisan	Mayıs	Haziran	Temmuz	Ağustos	Eylül
01	0.234	KURU	KURU	KURU	KURU	KURU	KURU	KURU	0.150	0.170	0.210	0.242
02	0.150	KURU	KURU	KURU	KURU	KURU	KURU	KURU	0.098	0.067	0.218	0.250
03	KURU	KURU	KURU	KURU	KURU	KURU	KURU	KURU	0.053	0.063	0.218	0.234
04	KURU	KURU	KURU	KURU	KURU	KURU	KURU	KURU	KURU	0.053	0.218	0.234
05	KURU	KURU	KURU	KURU	KURU	KURU	KURU	KURU	KURU	0.053	0.218	0.274
06	KURU	KURU	KURU	KURU	KURU	KURU	KURU	KURU	KURU	0.053	0.186	0.454
07	KURU	KURU	KURU	KURU	KURU	KURU	KURU	KURU	KURU	0.053	0.110	0.468
08	KURU	KURU	KURU	KURU	KURU	KURU	KURU	KURU	KURU	0.030	0.103	0.468
09	KURU	KURU	KURU	KURU	KURU	KURU	KURU	KURU	KURU	KURU	0.103	0.468
10	KURU	KURU	KURU	KURU	KURU	KURU	KURU	KURU	KURU	0.007	0.103	0.440
11	KURU	KURU	KURU	KURU	KURU	KURU	KURU	KURU	0.008	0.170	0.116	0.440
12	KURU	KURU	KURU	KURU	KURU	KURU	KURU	KURU	0.202	0.234	0.157	0.440
13	KURU	KURU	KURU	KURU	KURU	KURU	KURU	KURU	0.226	0.226	0.163	0.468
14	KURU	KURU	KURU	KURU	KURU	KURU	KURU	KURU	0.226	0.210	0.194	0.468
15	KURU	KURU	KURU	KURU	KURU	KURU	KURU	KURU	0.226	0.210	0.218	0.468
16	KURU	KURU	KURU	KURU	KURU	KURU	KURU	0.010	0.226	0.210	0.218	0.407
17	KURU	KURU	KURU	KURU	KURU	KURU	KURU	0.170	0.226	0.210	0.194	0.258
18	KURU	KURU	KURU	KURU	KURU	KURU	KURU	0.200	0.218	0.210	0.143	0.250
19	KURU	KURU	KURU	KURU	KURU	KURU	KURU	0.240	0.218	0.218	0.210	0.250
20	KURU	KURU	KURU	KURU	KURU	KURU	KURU	0.240	0.218	0.218	0.218	0.234
21	KURU	KURU	KURU	KURU	KURU	KURU	KURU	0.240	0.218	0.218	0.234	0.234
22	KURU	KURU	KURU	KURU	KURU	KURU	KURU	0.250	0.218	0.218	0.258	0.234
23	KURU	KURU	KURU	KURU	KURU	KURU	KURU	0.226	0.218	0.218	0.282	0.234
24	KURU	KURU	KURU	KURU	KURU	KURU	KURU	0.226	0.218	0.234	0.282	0.218
25	KURU	KURU	KURU	KURU	KURU	KURU	KURU	0.226	0.218	0.234	0.266	0.170
26	KURU	KURU	KURU	KURU	KURU	KURU	KURU	0.226	0.218	0.234	0.266	0.098
27	KURU	KURU	KURU	KURU	KURU	KURU	KURU	0.226	0.218	0.234	0.266	KURU
28	KURU	KURU	KURU	KURU	KURU	KURU	KURU	0.218	0.234	0.234	0.266	KURU
29	KURU	KURU	KURU	KURU	-----	KURU	KURU	0.186	0.234	0.234	0.266	KURU
30	KURU	KURU	KURU	KURU	-----	KURU	KURU	0.186	0.234	0.234	0.266	KURU
31	KURU	-----	KURU	KURU	-----	KURU	-----	0.186	-----	0.234	0.266	-----
Maks.	0.234	KURU	KURU	KURU	KURU	KURU	KURU	0.250	0.234	0.234	0.282	0.468
Min.	KURU	KURU	KURU	KURU	KURU	KURU	KURU	KURU	KURU	KURU	0.103	KURU
Ortalama	0.012	KURU	KURU	KURU	KURU	KURU	KURU	0.105	0.151	0.167	0.208	0.280
LT/SN/Km2	0.179	0.000	0.000	0.000	0.000	0.000	0.000	1.52	2.18	2.42	3.00	4.05
AKIM mm.	0.479	0.000	0.000	0.000	0.000	0.000	0.000	4.07	5.65	6.48	8.04	10.5
MİL. M3	0.033	0.000	0.000	0.000	0.000	0.000	0.000	0.281	0.391	0.449	0.556	0.726

SU YILI (2006) YILLIK TOPLAM AKIM 2.44 MİLYON M3 35 MM. 1.1 LT/SN/Km2

16. Konya Kapali Havzasi

D16A078 SUBERTE Ç. TAŞAĞIL

YERİ : **KONYA-SEYDİŞEHİR SEYDİŞEHİRDEN SORA ANTALYA YOLUNA DÖNÜLÜR 6 KM SONRA TAŞAĞIL KÖYÜNE DÖNÜLÜR TAŞAĞIL KÖYÜNDEN SORA 1 KM SONRA KÖPRÜ DE KURULU BİR İSTASYONDUR. 31°53'29" Doğu - 37°22'41" Kuzey**

YAĞIŞ ALANI : **111,80 km2** **YAKLAŞIK KOT : 1095 m**

GÖZLEM SÜRESİ : **22.04.1968 - 30.09.2006**

ORTALAMA AKIMLAR : **Gözlem süresinde 3.127 m3/sn. (32 Yıllık) 2006 Su yılında 2.787 m3/sn.**

ANLIK EN ÇOK VE EN AZ AKIMLAR:

2006 Su yılında anlık ençok akım	:	**36.3**	**m3/sn**	**12.02.2006**
2006 Su yılında anlık enaz akım	:	**0.000**	**m3/sn**	**04.09.2006**
Gözlem süresinde anlık ençok akım	:	**135.**	**m3/sn**	**13.12.1976**
Gözlem süresinde anlık enaz akım	:	**0.000**	**m3/sn**	**01.10.1975**

İstasyon için kullanılmış anahtar bulunamadı.

Akımlar 01 Ekim 2005 'den 30 Eylül 2006' a kadar m3/sn olarak

Gün	Ekim	Kasım	Aralık	Ocak	Şubat	Mart	Nisan	Mayıs	Haziran	Temmuz	Ağustos	Eylül
01	0.019	0.028	1.58	1.22	1.70	8.70	11.4	3.85	1.12	0.102	0.003	0.003
02	0.019	0.047	1.22	1.22	1.46	9.30	10.7	3.85	1.00	0.102	0.003	0.001
03	0.019	0.047	1.00	1.22	1.46	11.2	9.30	4.00	0.770	0.102	0.003	KURU
04	0.019	0.527	0.900	1.10	1.58	12.5	8.31	4.15	0.634	0.250	0.003	KURU
05	0.019	1.70	0.900	1.10	1.70	9.30	7.53	4.30	0.634	0.237	0.003	KURU
06	0.019	1.46	0.900	1.22	2.82	8.11	7.14	4.00	0.566	0.172	0.003	KURU
07	0.019	1.10	0.800	1.98	11.9	8.31	7.53	3.70	0.498	0.172	0.002	KURU
08	0.019	0.600	0.800	3.40	13.0	8.90	8.70	3.55	0.498	0.106	0.002	KURU
09	0.019	0.527	0.600	2.40	8.11	9.70	7.92	3.40	0.498	0.071	0.002	KURU
10	0.019	0.600	0.600	2.12	7.33	6.94	7.14	3.10	0.498	0.071	0.002	KURU
11	0.019	0.527	0.527	1.84	25.1	5.58	6.75	2.96	0.498	0.047	0.002	0.002
12	0.028	0.455	0.527	1.58	32.0	4.99	7.14	2.96	0.430	0.047	0.002	0.002
13	0.028	0.455	0.455	1.46	18.9	8.90	7.72	2.96	0.370	0.047	0.002	0.002
14	0.019	0.382	0.455	1.22	10.5	17.5	8.31	2.82	0.600	0.047	0.002	0.002
15	0.019	0.382	0.527	1.10	7.14	14.6	8.11	2.68	0.430	0.047	0.003	0.005
16	0.047	0.382	0.527	1.00	5.19	9.90	8.90	2.54	0.430	0.047	0.003	0.005
17	0.527	0.382	0.455	1.00	4.15	7.92	8.50	2.26	0.370	0.047	0.003	0.005
18	0.071	2.54	3.85	0.900	3.85	6.75	7.33	2.12	0.310	0.047	0.005	0.005
19	0.071	4.99	17.5	0.900	4.15	6.55	6.36	1.98	0.250	0.047	0.005	0.005
20	0.071	9.50	14.1	4.45	4.30	5.97	6.55	1.98	0.190	0.028	0.008	0.005
21	0.047	13.0	7.33	3.85	4.80	6.16	6.16	1.98	0.140	0.019	0.005	0.005
22	0.047	6.75	4.45	2.82	4.99	6.94	5.77	1.98	0.102	0.013	0.005	0.008
23	0.028	3.85	3.40	3.10	5.58	8.50	5.58	1.84	0.102	0.013	0.005	0.013
24	0.028	2.96	2.68	2.82	5.97	11.6	6.16	1.10	0.102	0.013	0.005	0.013
25	0.028	2.40	2.26	2.54	7.14	13.0	5.58	1.22	0.102	0.008	0.005	0.013
26	0.028	1.84	1.84	2.40	9.30	11.2	4.45	1.22	0.102	0.008	0.005	0.013
27	0.028	1.34	1.58	2.12	10.3	10.1	3.70	1.48	0.102	0.005	0.005	0.013
28	0.028	1.10	1.46	1.98	10.1	9.90	3.55	1.35	0.102	0.005	0.005	0.008
29	0.028	1.22	1.46	1.70	-----	9.70	3.70	1.12	0.102	0.003	0.005	0.008
30	0.019	1.46	1.46	1.84	-----	9.50	3.70	1.00	0.102	0.003	0.005	0.008
31	0.028	-----	1.34	1.84	-----	11.6	-----	1.12	-----	0.003	0.003	-----
Maks.	1.98	15.9	21.4	8.31	36.3	24.0	12.5	4.80	1.12	0.430	0.028	0.019
Min.	0.013	0.019	0.382	0.800	1.34	4.80	3.40	1.00	0.102	0.003	0.002	KURU
Ortalama	0.046	2.09	2.50	1.92	8.02	9.35	6.99	2.53	0.388	0.062	0.004	0.005
LT/SN/Km2	0.412	18.6	22.4	17.2	71.7	83.6	62.5	22.7	3.47	0.557	0.033	0.043
AKIM mm.	1.10	48.3	59.9	45.9	174.	224.	162.	60.7	9.00	1.49	0.088	0.111
MİL. M3	0.123	5.40	6.69	5.14	19.4	25.0	18.1	6.79	1.01	0.167	0.010	0.012

SU YILI (2006) YILLIK TOPLAM AKIM 87.84 MİLYON M3 786 MM. 24.9 LT/SN/Km2

16. Konya Kapali Havzasi

D16A080 Karasu Demirci

YERİ : **AKSARAY DEMİRCİ BELDESİ.**
34°16'47" Doğu - 38°23'19" Kuzey

YAĞIŞ ALANI : **497,38 km2** **YAKLAŞIK KOT : 1118 m**

GÖZLEM SÜRESİ : **17.11.1967 - 30.09.2006**

ORTALAMA AKIMLAR : **Gözlem süresinde 1.652 m3/sn. (35 Yıllık) 2006 Su yılında 0.879 m3/sn.**

ANLIK EN ÇOK VE EN AZ AKIMLAR:

2006 Su yılında anlık encok akım	**:**	**2.10**	**m3/sn**	**31.03.2006**
2006 Su yılında anlık enaz akım	**:**	**0.030**	**m3/sn**	**30.07.2006**
Gözlem süresinde anlık encok akım	**:**	**45.0**	**m3/sn**	**19.06.1981**
Gözlem süresinde anlık enaz akım	**:**	**0.000**	**m3/sn**	**02.06.1976**

İstasyon için kullanılmış anahtar bulunamadı.

Akımlar 01 Ekim 2005 'den 30 Eylül 2006' a kadar m3/sn olarak

Gün	Ekim	Kasım	Aralık	Ocak	Şubat	Mart	Nisan	Mayıs	Haziran	Temmuz	Ağustos	Eylül
01	0.440	1.23	1.23	1.74	1.59	1.43	2.00	1.05	0.070	0.130	0.030	0.130
02	0.440	1.23	1.23	1.74	1.59	1.43	2.00	1.05	0.070	0.130	0.030	0.130
03	0.440	1.23	1.23	1.74	1.59	1.43	2.00	1.05	0.070	0.130	0.030	0.130
04	0.440	1.23	1.23	1.74	1.59	1.43	2.00	1.05	0.070	0.130	0.030	0.130
05	0.456	1.23	1.23	1.74	1.59	1.43	2.00	1.05	0.070	0.030	0.030	0.130
06	0.456	1.23	1.23	1.74	1.59	1.43	2.00	1.05	0.070	0.030	0.030	0.130
07	0.456	1.23	1.23	1.74	1.59	1.43	2.00	1.05	0.070	0.030	0.030	0.130
08	0.280	1.23	1.23	1.74	1.59	1.43	1.30	1.05	0.070	0.030	0.030	0.130
09	0.280	1.23	1.23	1.74	1.59	1.43	1.30	1.05	0.070	0.030	0.030	0.130
10	0.456	1.23	1.23	1.74	1.43	1.43	1.30	1.05	0.119	0.030	0.030	0.200
11	0.280	1.23	1.43	1.74	1.43	1.43	1.30	1.05	0.119	0.030	0.030	0.200
12	0.544	1.23	1.43	1.74	1.43	1.43	1.30	1.05	0.119	0.030	0.030	0.200
13	0.632	1.23	1.43	1.74	1.43	1.43	1.30	1.05	0.119	0.030	0.030	0.270
14	0.720	1.23	1.43	1.74	1.43	1.43	1.30	0.368	0.119	0.030	0.030	0.270
15	0.720	1.23	1.43	1.74	1.33	1.43	1.15	0.280	0.200	0.030	0.073	0.270
16	0.821	1.23	1.43	1.74	1.33	1.43	1.05	0.280	0.200	0.030	0.073	0.270
17	0.821	1.23	1.43	1.74	1.43	1.43	1.05	0.280	0.200	0.030	0.073	0.270
18	0.821	1.23	1.43	1.74	1.43	1.43	1.05	0.280	0.200	0.030	0.073	0.270
19	0.821	1.23	1.43	1.74	1.43	1.43	1.15	0.280	0.200	0.030	0.073	0.200
20	0.821	1.23	1.43	1.74	1.43	1.43	1.15	0.168	0.200	0.030	0.073	0.200
21	0.720	1.23	1.43	1.74	1.43	1.43	0.940	0.168	0.200	0.030	0.030	0.200
22	0.720	1.23	1.43	1.74	1.59	1.43	1.05	0.168	0.200	0.030	0.030	0.200
23	0.821	1.23	1.43	1.74	1.59	2.10	1.05	0.168	0.200	0.030	0.030	0.200
24	1.33	1.23	1.74	1.74	1.33	2.10	1.05	0.168	0.200	0.030	0.030	0.200
25	1.43	1.23	1.74	1.74	1.33	2.10	1.15	0.168	0.200	0.030	0.030	0.200
26	1.43	1.23	1.74	1.74	1.33	2.10	1.15	0.070	0.200	0.030	0.030	0.200
27	1.43	1.23	1.74	1.74	1.33	2.10	0.940	0.070	0.200	0.030	0.030	0.270
28	1.33	1.23	1.74	1.74	1.33	2.10	0.940	0.070	0.130	0.030	0.030	0.270
29	1.33	1.23	1.74	1.74	-----	2.10	0.940	0.070	0.130	0.030	0.030	0.270
30	1.33	1.23	1.74	1.74	-----	2.10	0.940	0.070	0.130	0.030	0.030	0.270
31	1.33	-----	1.74	1.74	-----	2.10	-----	0.070	-----	0.030	0.030	-----
Maks.	1.43	1.23	1.74	1.74	1.59	2.10	2.00	1.05	0.200	0.130	0.073	0.270
Min.	0.280	1.23	1.23	1.74	1.33	1.43	0.940	0.070	0.070	0.030	0.030	0.130
Ortalama	0.785	1.23	1.45	1.74	1.47	1.62	1.33	0.543	0.141	0.043	0.038	0.202
LT/SN/Km2	1.58	2.47	2.91	3.50	2.95	3.27	2.67	1.09	0.282	0.086	0.077	0.407
AKIM mm.	4.23	6.41	7.78	9.37	7.14	8.75	6.92	2.93	0.732	0.231	0.206	1.05
MİL. M3	2.10	3.19	3.87	4.66	3.55	4.35	3.44	1.46	0.364	0.115	0.103	0.524

SU YILI (2006) YILLIK TOPLAM AKIM 27.73 MİLYON M3 56 MM. 1.8 LT/SN/Km2

16. Konya Kapali Havzasi

D16A081 Çigil D. Derivasyon Kan.

YERİ : **KONYA ILGIN**
31°53'32" Doğu - 38°16'46" Kuzey

YAĞIŞ ALANI : **622,10 km2** **YAKLAŞIK KOT : 1031 m**

GÖZLEM SÜRESİ : **01.12.1967 - 30.09.2006**

ORTALAMA AKIMLAR : **Gözlem süresinde 1.740 m3/sn. (36 Yıllık) 2006 Su yılında 1.247 m3/sn.**

ANLIK EN ÇOK VE EN AZ AKIMLAR:

2006 Su yılında anlık ençok akım	**:**	**41.2**	**m3/sn**	**24.04.2006**
2006 Su yılında anlık enaz akım	**:**	**0.000**	**m3/sn**	**01.10.2005**
Gözlem süresinde anlık ençok akım	**:**	**68.0**	**m3/sn**	**07.06.1972**
Gözlem süresinde anlık enaz akım	**:**	**0.000**	**m3/sn**	**01.10.1968**

İstasyon için kullanılmış anahtar bulunamadı.

Akımlar 01 Ekim 2005 'den 30 Eylül 2006' a kadar m3/sn olarak

Gün	Ekim	Kasım	Aralık	Ocak	Şubat	Mart	Nisan	Mayıs	Haziran	Temmuz	Ağustos	Eylül
01	KURU	0.001	0.782	0.782	0.818	3.30	3.15	2.32	0.964	0.440	KURU	KURU
02	KURU	0.003	0.747	0.782	0.818	3.15	3.01	4.80	0.856	0.400	KURU	KURU
03	KURU	0.005	0.782	0.782	0.818	3.15	2.80	6.60	0.748	0.138	KURU	KURU
04	KURU	0.043	0.747	0.782	0.818	3.22	2.68	4.60	0.676	0.088	KURU	KURU
05	KURU	0.028	0.747	0.818	0.747	2.73	2.62	7.00	0.676	KURU	KURU	KURU
06	KURU	0.035	0.782	0.888	0.782	2.56	2.50	5.70	0.480	KURU	KURU	KURU
07	KURU	0.090	0.818	0.853	1.03	2.56	2.44	4.70	0.300	KURU	KURU	KURU
08	KURU	0.227	0.818	0.853	1.14	2.67	2.38	4.60	0.088	KURU	KURU	KURU
09	KURU	0.243	0.818	0.853	1.14	2.78	2.38	5.20	0.022	KURU	KURU	KURU
10	KURU	0.276	0.818	0.853	1.06	2.56	2.80	4.40	0.022	KURU	KURU	KURU
11	KURU	0.295	0.818	0.818	1.34	2.45	2.50	4.00	0.022	KURU	KURU	KURU
12	KURU	0.276	0.782	0.818	2.14	2.45	2.26	3.50	0.045	KURU	KURU	KURU
13	KURU	0.408	0.747	0.818	2.40	2.94	1.68	3.36	0.065	KURU	KURU	KURU
14	KURU	0.351	0.747	0.818	2.04	5.30	0.640	3.15	0.029	KURU	KURU	KURU
15	KURU	0.550	0.747	0.782	1.81	5.60	0.640	3.01	0.022	KURU	KURU	KURU
16	KURU	0.550	0.782	0.782	1.50	5.90	1.72	2.94	0.022	KURU	KURU	KURU
17	KURU	0.494	0.747	0.782	1.59	6.10	0.964	3.08	0.011	KURU	KURU	KURU
18	KURU	0.522	0.747	0.782	1.63	5.30	0.166	3.01	0.001	KURU	KURU	KURU
19	KURU	0.607	0.782	0.747	1.94	5.90	0.166	2.68	KURU	KURU	KURU	KURU
20	KURU	0.663	0.818	0.818	2.09	5.60	0.166	2.56	KURU	KURU	KURU	KURU
21	KURU	1.14	0.747	0.782	2.78	5.00	0.166	2.38	KURU	KURU	KURU	KURU
22	KURU	0.959	0.747	0.782	2.73	4.70	0.166	2.16	KURU	KURU	KURU	KURU
23	KURU	0.818	0.747	0.853	2.56	4.30	0.166	2.00	KURU	KURU	KURU	KURU
24	KURU	0.782	0.719	0.888	2.56	4.40	26.3	1.80	KURU	KURU	KURU	KURU
25	KURU	0.747	0.719	0.853	2.89	4.20	19.1	1.68	KURU	KURU	KURU	KURU
26	KURU	0.747	0.691	0.853	3.22	4.00	9.05	1.60	KURU	KURU	KURU	KURU
27	KURU	0.782	0.747	0.853	3.67	3.70	7.80	1.76	KURU	KURU	KURU	KURU
28	0.001	0.782	0.747	0.818	3.59	3.43	5.60	1.52	KURU	KURU	KURU	KURU
29	0.001	0.818	0.747	0.818	-----	3.29	4.80	1.28	KURU	KURU	KURU	KURU
30	0.001	0.818	0.782	0.818	-----	3.15	4.20	1.04	0.400	KURU	KURU	KURU
31	0.001	-----	0.782	0.818	-----	3.08	-----	1.04	-----	KURU	KURU	-----
Maks.	0.003	1.46	0.888	0.959	4.04	6.80	41.2	15.3	1.00	0.440	KURU	KURU
Min.	KURU	0.001	0.635	0.747	0.691	2.45	0.166	0.784	KURU	KURU	KURU	KURU
Ortalama	0.000	0.469	0.766	0.818	1.84	3.85	3.83	3.21	0.182	0.034	KURU	KURU
LT/SN/Km2	0.000	0.753	1.23	1.31	2.97	6.19	6.16	5.16	0.292	0.055	0.000	0.000
AKIM mm.	0.001	1.95	3.30	3.52	7.17	16.6	16.0	13.8	0.757	0.148	0.000	0.000
MİL. M3	0.000	1.21	2.05	2.19	4.46	10.3	9.94	8.59	0.471	0.092	0.000	0.000

SU YILI (2006) YILLIK TOPLAM AKIM 39.30 MİLYON M3 63 MM. 2.0 LT/SN/Km2

16. Konya Kapali Havzasi

D16A087 Ayranci S. Kavaklik

YERİ : **KARAMAN AYRANCI.**
33°45'25" Doğu - 37°18'21" Kuzey

YAĞIŞ ALANI : **1137,10 km2** **YAKLAŞIK KOT : 1202 m**

GÖZLEM SÜRESİ : **17.09.1968 - 30.09.2006**

ORTALAMA AKIMLAR : **Gözlem süresinde 1.349 m3/sn. (32 Yıllık) 2006 Su yılında 0.511 m3/sn.**

ANLIK EN ÇOK VE EN AZ AKIMLAR:

2006 Su yılında anlık ençok akım	**:**	**24.8**	**m3/sn**	**29.06.2006**
2006 Su yılında anlık enaz akım	**:**	**0.000**	**m3/sn**	**10.10.2005**
Gözlem süresinde anlık ençok akım	**:**	**49.0**	**m3/sn**	**28.03.1980**
Gözlem süresinde anlık enaz akım	**:**	**0.000**	**m3/sn**	**14.06.1974**

1. Anahtar Eğrisi (Seviyeler cm olarak)

Seviye	Akım	Seviye	Akım	Seviye	Akım	Seviye	Akım
2	0.001	52	10.1	109	32.4	175	59.2
12	0.386	62	13.7	120	36.7	194	66.5
22	1.8	73	18.0	131	41.4	215	74.6
32	4.0	84	22.0	144	46.7	239	83.4
42	6.9	98	27.6	159	52.6		

Akımlar 01 Ekim 2005 'den 30 Eylül 2006' a kadar m3/sn olarak

Gün	Ekim	Kasım	Aralık	Ocak	Şubat	Mart	Nisan	Mayıs	Haziran	Temmuz	Ağustos	Eylül
01	KURU	0.023	0.050	0.023	0.010	0.047	3.32	0.960	0.047	4.42	KURU	KURU
02	KURU	0.037	0.050	0.037	0.010	1.63	3.58	0.960	KURU	3.58	KURU	KURU
03	KURU	0.037	0.050	0.037	0.010	2.20	3.32	0.960	KURU	1.63	KURU	KURU
04	KURU	0.037	0.050	0.037	0.010	2.20	3.06	0.960	KURU	0.740	KURU	KURU
05	KURU	0.037	0.050	0.037	0.010	2.20	3.06	0.960	KURU	0.630	KURU	KURU
06	KURU	0.037	0.050	0.037	0.023	2.00	3.06	0.740	KURU	0.019	KURU	KURU
07	KURU	0.037	0.050	0.050	0.088	2.20	3.06	0.740	0.010	KURU	KURU	KURU
08	KURU	0.037	0.050	0.050	0.088	2.80	3.32	0.630	0.019	KURU	KURU	KURU
09	KURU	0.037	0.050	0.050	0.088	2.40	3.06	0.524	0.031	KURU	KURU	KURU
10	KURU	0.050	0.037	0.050	0.088	1.80	3.58	0.524	0.019	KURU	KURU	KURU
11	KURU	0.050	0.037	0.050	0.064	1.63	3.84	0.417	0.019	KURU	KURU	KURU
12	KURU	0.050	0.023	0.050	0.064	1.30	3.58	0.349	0.019	KURU	KURU	KURU
13	KURU	0.050	0.023	0.050	0.064	1.13	3.58	0.282	0.019	KURU	KURU	KURU
14	KURU	0.050	0.023	0.050	0.064	1.46	3.32	0.282	0.010	KURU	KURU	KURU
15	KURU	0.050	0.037	0.050	0.064	1.46	3.06	0.282	0.001	KURU	KURU	KURU
16	KURU	0.050	0.037	0.050	0.064	1.30	3.06	0.282	KURU	KURU	KURU	KURU
17	KURU	0.050	0.037	0.023	0.064	1.30	3.06	0.524	KURU	KURU	KURU	KURU
18	KURU	0.050	0.037	0.007	0.064	1.46	3.06	0.630	KURU	KURU	KURU	KURU
19	0.470	0.050	0.037	0.007	0.064	1.80	2.60	0.417	KURU	KURU	KURU	KURU
20	0.800	0.050	0.050	0.023	0.064	1.80	2.40	0.047	KURU	KURU	KURU	KURU
21	0.800	0.140	0.080	0.023	0.047	1.63	2.20	0.031	KURU	KURU	KURU	KURU
22	0.250	0.470	0.110	0.010	0.047	1.80	2.00	0.168	KURU	KURU	KURU	KURU
23	0.023	0.140	0.110	0.004	0.047	2.60	1.80	0.214	KURU	KURU	KURU	KURU
24	0.023	0.050	0.080	0.007	0.031	3.06	1.63	0.214	KURU	KURU	KURU	KURU
25	0.023	0.050	0.080	0.007	0.031	3.58	1.80	0.214	KURU	KURU	KURU	KURU
26	0.023	0.050	0.080	0.010	0.031	3.32	1.63	0.168	KURU	KURU	KURU	KURU
27	0.023	0.050	0.080	0.010	0.031	3.06	1.13	0.088	KURU	KURU	KURU	KURU
28	0.023	0.050	0.050	0.010	0.031	3.06	1.13	0.088	KURU	KURU	KURU	KURU
29	0.023	0.050	0.010	0.010	-----	3.06	1.13	0.088	0.088	KURU	KURU	KURU
30	0.023	0.050	0.010	0.010	-----	3.06	1.13	0.064	8.98	KURU	KURU	KURU
31	0.023	-----	0.023	0.010	-----	3.32	-----	0.064	-----	KURU	KURU	-----
Maks.	1.02	0.580	0.140	0.050	0.088	3.58	4.42	3.84	24.8	4.74	KURU	KURU
Min.	KURU	0.023	0.010	0.004	0.010	0.031	0.960	0.031	KURU	KURU	KURU	KURU
Ortalama	0.082	0.066	0.050	0.028	0.049	2.12	2.65	0.415	0.309	0.355	KURU	KURU
LT/SN/Km2	0.072	0.058	0.044	0.025	0.043	1.86	2.33	0.365	0.272	0.313	0.000	0.000
AKIM mm.	0.192	0.150	0.117	0.067	0.103	4.99	6.05	0.978	0.704	0.837	0.000	0.000
MİL. M3	0.218	0.170	0.133	0.076	0.118	5.67	6.87	1.11	0.800	0.952	0.000	0.000

SU YILI (2006) YILLIK TOPLAM AKIM 16.12 MİLYON M3 14 MM. 0.4 LT/SN/Km2

16. Konya Kapali Havzasi

D16A089 Uzandi D. Kirkpinar Köp.

YERİ : **NİĞDE YEŞİLBURÇ KÖYÜ KIRKPINAR KÖPRÜSÜ.**
34°39'47" Doğu - 38°2'55" Kuzey

YAĞIŞ ALANI : **21,30 km2** **YAKLAŞIK KOT : 1474 m**

GÖZLEM SÜRESİ : **10.03.1970 - 30.09.2006**

ORTALAMA AKIMLAR : **Gözlem süresinde 0.120 m3/sn. (26 Yıllık) 2006 Su yılında 0.079 m3/sn.**

ANLIK EN ÇOK VE EN AZ AKIMLAR:

2006 Su yılında anlık ençok akım	**:**	**0.550**	**m3/sn**	**03.07.2006**
2006 Su yılında anlık enaz akım	**:**	**0.000**	**m3/sn**	**11.02.2006**
Gözlem süresinde anlık ençok akım	**:**	**5.80**	**m3/sn**	**10.06.1999**
Gözlem süresinde anlık enaz akım	**:**	**0.000**	**m3/sn**	**01.10.1972**

İstasyon için kullanılmış anahtar bulunamadı.

Akımlar 01 Ekim 2005 'den 30 Eylül 2006' a kadar m3/sn olarak

Gün	Ekim	Kasım	Aralık	Ocak	Şubat	Mart	Nisan	Mayıs	Haziran	Temmuz	Ağustos	Eylül
01	0.085	0.016	0.009	0.112	0.007	0.015	0.018	0.029	0.053	0.238	0.177	0.177
02	0.075	0.016	0.009	0.016	0.007	0.015	0.036	0.043	0.138	0.238	0.177	0.177
03	0.085	0.016	0.009	0.009	0.005	0.018	0.022	0.036	0.190	0.262	0.177	0.190
04	0.075	0.019	0.009	0.009	0.005	0.022	0.022	0.029	0.177	0.214	0.177	0.177
05	0.085	0.016	0.012	0.009	0.005	0.018	0.018	0.029	0.177	0.238	0.177	0.177
06	0.085	0.016	0.012	0.009	0.005	0.018	0.018	0.022	0.164	0.238	0.177	0.177
07	0.085	0.016	0.009	0.009	0.005	0.018	0.018	0.029	0.177	0.214	0.214	0.177
08	0.009	0.016	0.009	0.009	0.004	0.018	0.022	0.036	0.190	0.214	0.190	0.177
09	0.012	0.016	0.009	0.016	0.001	0.018	0.022	0.036	0.190	0.214	0.190	0.177
10	0.012	0.016	0.009	0.043	KURU	0.015	0.029	0.029	0.177	0.238	0.190	0.177
11	0.012	0.016	0.009	0.007	KURU	0.015	0.029	0.029	0.190	0.238	0.190	0.177
12	0.012	0.016	0.012	0.028	KURU	0.015	0.029	0.036	0.190	0.238	0.190	0.164
13	0.012	0.016	0.019	0.012	0.022	0.015	0.029	0.036	0.164	0.238	0.190	0.164
14	0.012	0.016	0.012	0.009	0.015	0.015	0.036	0.029	0.177	0.238	0.214	0.177
15	0.012	0.016	0.012	0.009	0.018	0.015	0.029	0.029	0.190	0.238	0.214	0.164
16	0.012	0.016	0.012	0.009	0.018	0.015	0.036	0.036	0.190	0.214	0.214	0.164
17	0.012	0.012	0.012	0.009	0.018	0.018	0.036	0.036	0.177	0.214	0.238	0.151
18	0.012	0.012	0.012	0.009	0.018	0.022	0.029	0.029	0.177	0.214	0.214	0.138
19	0.012	0.016	0.009	0.028	0.015	0.036	0.022	0.029	0.177	0.238	0.214	0.138
20	0.012	0.016	0.007	0.100	0.015	0.029	0.022	0.029	0.164	0.190	0.214	0.151
21	0.016	0.016	0.007	0.051	0.015	0.022	0.036	0.029	0.164	0.177	0.190	0.151
22	0.016	0.012	0.012	0.028	0.018	0.022	0.036	0.036	0.177	0.177	0.190	0.151
23	0.016	0.016	0.063	0.019	0.018	0.022	0.036	0.036	0.177	0.177	0.190	0.151
24	0.016	0.016	0.100	0.016	0.018	0.022	0.036	0.036	0.177	0.177	0.214	0.138
25	0.016	0.012	0.100	0.012	0.018	0.022	0.029	0.036	0.190	0.177	0.214	0.103
26	0.016	0.012	0.100	0.012	0.018	0.022	0.018	0.029	0.190	0.177	0.214	0.069
27	0.016	0.012	0.175	0.012	0.018	0.022	0.015	0.029	0.177	0.177	0.190	0.062
28	0.016	0.012	0.217	0.009	0.018	0.018	0.011	0.022	0.214	0.177	0.190	0.054
29	0.016	0.012	0.247	0.009	-----	0.018	0.018	0.029	0.262	0.177	0.177	0.047
30	0.016	0.012	0.247	0.007	-----	0.018	0.018	0.029	0.286	0.177	0.177	0.039
31	0.016	-----	0.247	0.007	-----	0.022	-----	0.022	-----	0.177	0.177	-----
Maks.	0.085	0.028	0.247	0.247	0.029	0.053	0.043	0.053	0.460	0.550	0.286	0.190
Min.	0.007	0.007	0.007	0.007	KURU	0.011	0.006	0.015	0.015	0.164	0.164	0.032
Ortalama	0.029	0.015	0.056	0.021	0.012	0.019	0.026	0.031	0.181	0.210	0.196	0.145
LT/SN/Km2	1.37	0.700	2.62	0.974	0.543	0.909	1.21	1.47	8.52	9.87	9.18	6.79
AKIM mm.	3.67	1.81	7.01	2.61	1.31	2.43	3.14	3.93	22.1	26.4	24.6	17.6
MİL. M3	0.078	0.039	0.149	0.056	0.028	0.052	0.067	0.084	0.470	0.563	0.524	0.375

SU YILI (2006) YILLIK TOPLAM AKIM 2.49 MİLYON M3 117 MM. 3.7 LT/SN/Km2

16. Konya Kapali Havzasi

D16A092 Kale Reg. Giris (Zaferiye Köp.)

YERİ : **ZAFERİYE KÖYÜ ILGIN/KONYA**
32°2'53" Doğu - 38°18'51" Kuzey

YAĞIŞ ALANI : **1696,10 km2** **YAKLAŞIK KOT : 1015 m**

GÖZLEM SÜRESİ : **12.10.1970 - 30.09.2006**

ORTALAMA AKIMLAR : **Gözlem süresinde 3.413 m3/sn. (35 Yıllık) 2006 Su yılında 1.665 m3/sn.**

ANLIK EN ÇOK VE EN AZ AKIMLAR:

2006 Su yılında anlık ençok akım	**:**	**8.08**	**m3/sn**	**02.05.2006**
2006 Su yılında anlık enaz akım	**:**	**0.088**	**m3/sn**	**11.08.2006**
Gözlem süresinde anlık ençok akım	**:**	**58.0**	**m3/sn**	**14.12.1976**
Gözlem süresinde anlık enaz akım	**:**	**0.000**	**m3/sn**	**01.10.1974**

İstasyon için kullanılmış anahtar bulunamadı.

Akımlar 01 Ekim 2005 'den 30 Eylül 2006' a kadar m3/sn olarak

Gün	Ekim	Kasım	Aralık	Ocak	Şubat	Mart	Nisan	Mayıs	Haziran	Temmuz	Ağustos	Eylül
01	0.700	0.784	1.17	0.940	0.800	1.01	0.870	5.73	2.60	4.53	0.520	0.190
02	0.700	0.784	1.17	0.870	0.800	1.01	0.940	6.38	2.30	4.39	0.450	1.15
03	0.700	0.912	1.17	0.800	0.870	0.940	0.940	6.12	2.06	3.90	0.450	1.15
04	0.700	1.30	1.10	0.800	0.870	0.940	0.940	6.26	2.06	2.95	0.450	0.590
05	0.700	1.30	1.17	0.730	0.730	0.940	0.870	6.26	2.06	1.84	0.450	1.01
06	1.48	1.45	1.17	0.730	0.800	1.01	0.870	6.08	2.06	1.30	0.450	0.800
07	2.25	1.23	1.10	0.730	0.800	0.940	0.800	6.16	2.06	1.22	0.450	0.320
08	2.25	1.17	1.30	0.730	0.870	0.870	0.800	6.16	2.06	1.22	0.800	0.520
09	2.17	1.17	1.17	0.730	0.870	0.800	0.800	6.38	2.14	1.15	0.450	0.520
10	2.25	1.10	1.04	0.730	0.870	0.730	0.800	6.20	2.14	1.15	0.190	0.590
11	2.34	1.04	0.784	0.730	0.870	0.660	0.800	6.26	2.14	1.08	0.088	0.590
12	2.51	1.04	0.660	0.730	0.800	0.660	0.730	6.26	2.14	1.01	0.450	0.870
13	2.60	0.912	0.660	0.730	0.800	0.660	0.730	6.50	2.14	1.08	0.380	1.01
14	2.68	0.848	0.720	0.730	0.870	0.730	1.84	6.38	2.14	1.01	0.190	1.01
15	2.60	0.848	0.784	0.660	1.01	0.800	2.14	6.26	2.14	0.940	0.190	0.870
16	2.76	0.848	0.848	0.660	1.01	0.800	1.66	6.32	2.14	0.800	0.190	0.660
17	2.76	0.912	0.912	0.660	0.940	0.800	1.52	6.44	2.14	0.800	0.260	0.870
18	0.784	0.976	2.22	0.730	0.940	0.870	1.60	6.38	2.14	1.22	0.190	1.22
19	0.848	1.04	2.36	0.730	1.01	0.870	1.45	6.32	2.14	1.52	0.870	1.37
20	0.848	1.10	2.42	0.730	0.940	0.800	1.78	6.20	2.06	1.52	1.22	1.52
21	0.848	1.36	0.940	0.730	1.45	0.870	2.06	6.20	2.06	1.45	1.08	1.52
22	0.848	1.23	0.940	0.730	1.30	0.870	2.67	6.16	1.98	1.45	1.08	1.84
23	0.848	1.23	0.870	0.730	1.30	0.940	2.81	6.16	1.98	1.45	0.660	1.98
24	0.848	1.17	0.870	0.730	1.22	0.940	4.39	6.08	1.98	1.45	1.30	1.98
25	0.912	1.17	0.800	0.800	1.15	0.870	5.10	6.04	1.90	1.45	1.22	1.98
26	0.848	1.17	0.800	0.800	1.08	0.940	4.04	4.85	1.90	1.37	1.15	1.98
27	0.660	1.17	0.800	0.800	1.01	0.940	3.23	5.66	1.90	1.45	1.37	1.90
28	0.660	1.17	0.870	0.800	1.01	0.940	5.88	6.00	1.90	1.37	1.30	1.98
29	0.720	1.17	0.940	0.800	-----	0.940	5.66	6.00	2.88	0.800	0.800	1.98
30	0.720	1.17	0.940	0.800	-----	0.870	5.59	6.00	2.88	0.730	0.260	1.90
31	0.848	-----	0.940	0.800	-----	0.870	-----	4.65	-----	0.590	0.320	-----
Maks.	2.84	1.71	2.42	1.01	1.60	1.01	6.32	8.08	5.17	4.60	1.52	2.30
Min.	0.660	0.720	0.660	0.660	0.730	0.660	0.660	2.74	1.90	0.520	0.088	0.190
Ortalama	1.40	1.09	1.09	0.755	0.964	0.865	2.14	6.09	2.14	1.55	0.620	1.20
LT/SN/Km2	0.825	0.644	0.640	0.445	0.568	0.510	1.26	3.59	1.26	0.917	0.366	0.705
AKIM mm.	2.21	1.67	1.71	1.19	1.37	1.37	3.28	9.62	3.27	2.45	0.979	1.83
MİL. M3	3.75	2.83	2.91	2.02	2.33	2.32	5.56	16.3	5.55	4.16	1.66	3.10

SU YILI (2006) YILLIK TOPLAM AKIM 52.49 MİLYON M3 31 MM. 1.0 LT/SN/Km2

16. Konya Kapali Havzasi

D16A094 Gümüsler Brj. Giris

YERİ : **NİĞDE GÜMÜŞLER BELDESİ.**
34°47'7" Doğu - 38°0'36" Kuzey

YAĞIŞ ALANI : **57,30 km2** **YAKLAŞIK KOT : 1376 m**

GÖZLEM SÜRESİ : **20.07.1970 - 30.09.2006**

ORTALAMA AKIMLAR : **Gözlem süresinde 0.135 m3/sn. (29 Yıllık) 2006 Su yılında 0.103 m3/sn.**

ANLIK EN ÇOK VE EN AZ AKIMLAR:

2006 Su yılında anlık encok akım	**:**	**0.386 m3/sn**	**03.05.2006**
2006 Su yılında anlık enaz akım	**:**	**0.000 m3/sn**	**01.10.2005**
Gözlem süresinde anlık encok akım	**:**	**1.30 m3/sn**	**08.04.1980**
Gözlem süresinde anlık enaz akım	**:**	**0.000 m3/sn**	**01.10.1975**

İstasyon için kullanılmış anahtar bulunamadı.

Akımlar 01 Ekim 2005 'den 30 Eylül 2006' a kadar m3/sn olarak

Gün	Ekim	Kasım	Aralık	Ocak	Şubat	Mart	Nisan	Mayıs	Haziran	Temmuz	Ağustos	Eylül
01	KURU	0.115	0.115	0.140	0.160	0.185	0.185	0.290	KURU	KURU	KURU	KURU
02	KURU	0.115	0.115	0.140	0.140	0.160	0.210	0.350	KURU	KURU	KURU	KURU
03	0.001	0.140	0.115	0.140	0.140	0.160	0.185	0.386	KURU	KURU	KURU	KURU
04	0.062	0.160	0.115	0.140	0.140	0.140	0.185	0.350	KURU	KURU	KURU	KURU
05	0.078	0.160	0.115	0.140	0.160	0.140	0.185	0.350	KURU	KURU	KURU	KURU
06	0.078	0.160	0.115	0.115	0.200	0.140	0.185	0.350	KURU	KURU	KURU	KURU
07	0.078	0.160	0.115	0.115	0.350	0.140	0.185	0.290	KURU	KURU	KURU	KURU
08	0.078	0.160	0.115	0.140	0.350	0.140	0.185	0.290	KURU	KURU	KURU	KURU
09	0.078	0.140	0.115	0.140	0.350	0.140	0.185	0.290	KURU	KURU	KURU	KURU
10	0.095	0.140	0.115	0.140	0.290	0.140	0.185	0.290	KURU	KURU	KURU	KURU
11	0.095	0.140	0.115	0.140	0.290	0.140	0.185	0.290	KURU	KURU	KURU	KURU
12	0.095	0.140	0.140	0.140	0.240	0.140	0.185	0.290	KURU	KURU	KURU	KURU
13	0.095	0.140	0.140	0.140	0.240	0.140	0.185	0.325	KURU	KURU	KURU	KURU
14	0.095	0.140	0.140	0.160	0.210	0.140	0.185	0.290	KURU	KURU	KURU	KURU
15	0.095	0.140	0.140	0.160	0.240	0.185	0.185	0.290	KURU	KURU	KURU	KURU
16	0.095	0.140	0.140	0.140	0.240	0.185	0.185	0.185	KURU	KURU	KURU	KURU
17	0.115	0.140	0.140	0.140	0.240	0.185	0.185	0.002	KURU	KURU	KURU	KURU
18	0.115	0.140	0.140	0.115	0.185	0.210	0.185	KURU	KURU	KURU	KURU	KURU
19	0.115	0.115	0.140	0.140	0.160	0.210	0.185	KURU	KURU	KURU	KURU	KURU
20	0.115	0.115	0.140	0.160	0.140	0.185	0.185	KURU	KURU	KURU	KURU	KURU
21	0.115	0.115	0.140	0.180	0.140	0.185	0.185	KURU	KURU	KURU	KURU	KURU
22	0.115	0.115	0.140	0.200	0.140	0.185	0.185	KURU	KURU	KURU	KURU	KURU
23	0.115	0.115	0.140	0.200	0.160	0.185	0.185	KURU	KURU	KURU	KURU	KURU
24	0.115	0.115	0.140	0.200	0.160	0.185	0.210	KURU	KURU	KURU	KURU	KURU
25	0.115	0.115	0.115	0.180	0.160	0.185	0.270	KURU	KURU	KURU	KURU	KURU
26	0.115	0.115	0.115	0.180	0.160	0.185	0.270	KURU	KURU	KURU	KURU	KURU
27	0.115	0.115	0.115	0.160	0.160	0.185	0.290	KURU	KURU	KURU	KURU	KURU
28	0.115	0.115	0.140	0.160	0.160	0.185	0.290	KURU	KURU	KURU	KURU	KURU
29	0.115	0.115	0.140	0.160	-----	0.185	0.290	KURU	KURU	KURU	KURU	KURU
30	0.115	0.115	0.140	0.160	-----	0.185	0.270	KURU	KURU	KURU	KURU	KURU
31	0.115	-----	0.140	0.160	-----	0.185	-----	KURU	-----	KURU	KURU	-----
Maks.	0.140	0.180	0.160	0.200	0.350	0.210	0.290	0.386	KURU	KURU	KURU	KURU
Min.	KURU	0.095	0.095	0.115	0.140	0.140	0.185	KURU	KURU	KURU	KURU	KURU
Ortalama	0.092	0.132	0.129	0.152	0.204	0.169	0.206	0.158	KURU	KURU	KURU	KURU
LT/SN/Km2	1.60	2.30	2.25	2.66	3.56	2.95	3.59	2.76	0.000	0.000	0.000	0.000
AKIM mm.	4.29	5.96	6.02	7.12	8.60	7.90	9.30	7.40	0.000	0.000	0.000	0.000
MİL. M3	0.246	0.341	0.345	0.408	0.493	0.453	0.533	0.424	0.000	0.000	0.000	0.000

SU YILI (2006) YILLIK TOPLAM AKIM 3.24 MİLYON M3 57 MM. 1.8 LT/SN/Km2

16. Konya Kapali Havzasi

D16A095 Apa Brj. Çikis

YERİ : **ÇUMRA APA BELDESİ.**
32°33'27" Doğu - 37°22'24" Kuzey

YAĞIŞ ALANI : **6795,00 km2** **YAKLAŞIK KOT : 1026 m**

GÖZLEM SÜRESİ : **01.04.1970 - 30.09.2006**

ORTALAMA AKIMLAR : **Gözlem süresinde 10.947 m3/sn. (35 Yıllık) 2006 Su yılında 3.893 m3/sn.**

ANLIK EN ÇOK VE EN AZ AKIMLAR:

2006 Su yılında anlık ençok akım	**:**	**45.2**	**m3/sn**	**22.04.2006**
2006 Su yılında anlık enaz akım	**:**	**0.000**	**m3/sn**	**01.10.2005**
Gözlem süresinde anlık ençok akım	**:**	**74.8**	**m3/sn**	**26.06.2003**
Gözlem süresinde anlık enaz akım	**:**	**0.000**	**m3/sn**	**10.09.1974**

İstasyon için kullanılmış anahtar bulunamadı.

Akımlar 01 Ekim 2005 'den 30 Eylül 2006' a kadar m3/sn olarak

Gün	Ekim	Kasım	Aralık	Ocak	Şubat	Mart	Nisan	Mayıs	Haziran	Temmuz	Ağustos	Eylül
01	KURU	KURU	KURU	KURU	KURU	KURU	KURU	31.4	KURU	20.0	KURU	KURU
02	KURU	KURU	KURU	KURU	KURU	KURU	KURU	30.8	KURU	19.2	KURU	KURU
03	KURU	KURU	KURU	KURU	KURU	KURU	KURU	30.8	KURU	24.5	KURU	KURU
04	KURU	KURU	KURU	KURU	KURU	KURU	KURU	31.4	KURU	29.1	KURU	KURU
05	KURU	KURU	KURU	KURU	KURU	KURU	KURU	30.8	KURU	25.8	KURU	KURU
06	KURU	KURU	KURU	KURU	KURU	KURU	KURU	30.3	KURU	24.1	KURU	KURU
07	KURU	KURU	KURU	KURU	KURU	KURU	1.99	29.7	KURU	22.5	KURU	KURU
08	KURU	KURU	KURU	KURU	KURU	KURU	33.7	23.3	KURU	20.4	KURU	KURU
09	KURU	KURU	KURU	KURU	KURU	KURU	34.9	16.3	KURU	18.3	KURU	KURU
10	KURU	KURU	KURU	KURU	KURU	KURU	34.9	13.4	KURU	0.067	KURU	KURU
11	KURU	KURU	KURU	KURU	KURU	KURU	34.9	5.22	KURU	KURU	KURU	KURU
12	KURU	KURU	KURU	KURU	KURU	KURU	37.8	KURU	KURU	KURU	KURU	KURU
13	KURU	KURU	KURU	KURU	KURU	KURU	41.8	KURU	KURU	KURU	KURU	KURU
14	KURU	KURU	KURU	KURU	KURU	KURU	43.5	KURU	KURU	KURU	KURU	KURU
15	KURU	KURU	KURU	KURU	KURU	KURU	43.5	KURU	KURU	KURU	KURU	KURU
16	KURU	KURU	KURU	KURU	KURU	KURU	43.5	KURU	KURU	KURU	KURU	KURU
17	KURU	KURU	KURU	KURU	KURU	KURU	43.5	KURU	KURU	KURU	KURU	KURU
18	KURU	KURU	KURU	KURU	KURU	KURU	38.3	KURU	KURU	KURU	KURU	KURU
19	KURU	KURU	KURU	KURU	KURU	KURU	32.0	KURU	KURU	KURU	KURU	KURU
20	KURU	KURU	KURU	KURU	KURU	KURU	32.6	KURU	KURU	KURU	KURU	KURU
21	KURU	KURU	KURU	KURU	KURU	KURU	32.0	KURU	KURU	KURU	KURU	KURU
22	KURU	KURU	KURU	KURU	KURU	KURU	35.5	KURU	KURU	KURU	KURU	KURU
23	KURU	KURU	KURU	KURU	KURU	KURU	34.3	KURU	KURU	KURU	KURU	KURU
24	KURU	KURU	KURU	KURU	KURU	KURU	34.9	KURU	KURU	KURU	KURU	KURU
25	KURU	KURU	KURU	KURU	KURU	KURU	34.9	KURU	KURU	KURU	KURU	KURU
26	KURU	KURU	KURU	KURU	KURU	KURU	34.3	KURU	1.84	KURU	KURU	KURU
27	KURU	KURU	KURU	KURU	KURU	KURU	33.7	KURU	24.5	KURU	KURU	KURU
28	KURU	KURU	KURU	KURU	KURU	KURU	33.2	KURU	20.8	7.98	KURU	KURU
29	KURU	KURU	KURU	KURU	-----	KURU	32.6	KURU	20.8	12.1	KURU	KURU
30	KURU	KURU	KURU	KURU	-----	KURU	32.0	KURU	20.8	0.280	KURU	KURU
31	KURU	-----	KURU	KURU	-----	KURU	-----	KURU	-----	KURU	KURU	-----
Maks.	KURU	KURU	KURU	KURU	KURU	KURU	45.2	32.0	33.2	30.8	KURU	KURU
Min.	KURU	KURU	KURU	KURU	KURU	KURU	KURU	KURU	KURU	KURU	KURU	KURU
Ortalama	KURU	KURU	KURU	KURU	KURU	KURU	27.8	8.82	2.96	7.24	KURU	KURU
LT/SN/Km2	0.000	0.000	0.000	0.000	0.000	0.000	4.09	1.30	0.435	1.06	0.000	0.000
AKIM mm.	0.000	0.000	0.000	0.000	0.000	0.000	10.6	3.48	1.13	2.85	0.000	0.000
MİL. M3	0.000	0.000	0.000	0.000	0.000	0.000	72.1	23.6	7.67	19.4	0.000	0.000

SU YILI (2006) YILLIK TOPLAM AKIM 122.77 MİLYON M3 18 MM. 0.6 LT/SN/Km2

16. Konya Kapali Havzasi

D16A096 Alkaran Sul.Kan. Apa Brj.

YERİ : **ÇUMRA APA BELDESİ.**
32°33'3" Doğu - 37°21'41" Kuzey

YAĞIŞ ALANI : **6795,00 km2** **YAKLAŞIK KOT : 1027 m**

GÖZLEM SÜRESİ : **18.05.1971 - 30.09.2006**

ORTALAMA AKIMLAR : **Gözlem süresinde 0.558 m3/sn. (27 Yıllık) 2006 Su yılında 0.332 m3/sn.**

ANLIK EN ÇOK VE EN AZ AKIMLAR:

2006 Su yılında anlık encok akım	**:**	**5.44**	**m3/sn**	**22.04.2006**
2006 Su yılında anlık enaz akım	**:**	**0.000**	**m3/sn**	**01.10.2005**
Gözlem süresinde anlık encok akım	**:**	**5.77**	**m3/sn**	**29.07.2002**
Gözlem süresinde anlık enaz akım	**:**	**0.000**	**m3/sn**	**01.10.1971**

İstasyon için kullanılmış anahtar bulunamadı.

Akımlar 01 Ekim 2005 'den 30 Eylül 2006' a kadar m3/sn olarak

Gün	Ekim	Kasım	Aralık	Ocak	Şubat	Mart	Nisan	Mayıs	Haziran	Temmuz	Ağustos	Eylül
01	KURU	KURU	KURU	KURU	KURU	KURU	KURU	4.27	KURU	1.54	KURU	KURU
02	KURU	KURU	KURU	KURU	KURU	KURU	KURU	4.37	KURU	1.78	KURU	KURU
03	KURU	KURU	KURU	KURU	KURU	KURU	KURU	3.10	KURU	2.65	KURU	KURU
04	KURU	KURU	KURU	KURU	KURU	KURU	KURU	2.23	KURU	2.78	KURU	KURU
05	KURU	KURU	KURU	KURU	KURU	KURU	KURU	2.00	KURU	2.71	KURU	KURU
06	KURU	KURU	KURU	KURU	KURU	KURU	KURU	2.00	KURU	2.45	KURU	KURU
07	KURU	KURU	KURU	KURU	KURU	KURU	KURU	2.00	KURU	2.30	KURU	KURU
08	KURU	KURU	KURU	KURU	KURU	KURU	KURU	1.85	KURU	1.54	KURU	KURU
09	KURU	KURU	KURU	KURU	KURU	KURU	KURU	1.59	KURU	1.17	KURU	KURU
10	KURU	KURU	KURU	KURU	KURU	KURU	KURU	1.44	KURU	0.150	KURU	KURU
11	KURU	KURU	KURU	KURU	KURU	KURU	KURU	1.09	KURU	KURU	KURU	KURU
12	KURU	KURU	KURU	KURU	KURU	KURU	KURU	0.005	KURU	KURU	KURU	KURU
13	KURU	KURU	KURU	KURU	KURU	KURU	KURU	KURU	KURU	KURU	KURU	KURU
14	KURU	KURU	KURU	KURU	KURU	KURU	KURU	KURU	KURU	KURU	KURU	KURU
15	KURU	KURU	KURU	KURU	KURU	KURU	KURU	KURU	KURU	KURU	KURU	KURU
16	KURU	KURU	KURU	KURU	KURU	KURU	KURU	KURU	KURU	KURU	KURU	KURU
17	KURU	KURU	KURU	KURU	KURU	KURU	KURU	KURU	KURU	KURU	KURU	KURU
18	KURU	KURU	KURU	KURU	KURU	KURU	KURU	KURU	KURU	KURU	KURU	KURU
19	KURU	KURU	KURU	KURU	KURU	KURU	0.760	KURU	KURU	KURU	KURU	KURU
20	KURU	KURU	KURU	KURU	KURU	KURU	5.00	KURU	KURU	KURU	KURU	KURU
21	KURU	KURU	KURU	KURU	KURU	KURU	5.00	KURU	KURU	KURU	KURU	KURU
22	KURU	KURU	KURU	KURU	KURU	KURU	5.44	KURU	KURU	KURU	KURU	KURU
23	KURU	KURU	KURU	KURU	KURU	KURU	5.33	KURU	KURU	KURU	KURU	KURU
24	KURU	KURU	KURU	KURU	KURU	KURU	4.90	KURU	KURU	KURU	KURU	KURU
25	KURU	KURU	KURU	KURU	KURU	KURU	4.69	KURU	KURU	KURU	KURU	KURU
26	KURU	KURU	KURU	KURU	KURU	KURU	4.48	KURU	0.010	KURU	KURU	KURU
27	KURU	KURU	KURU	KURU	KURU	KURU	4.69	KURU	3.87	0.286	KURU	KURU
28	KURU	KURU	KURU	KURU	KURU	KURU	4.79	KURU	4.79	2.30	KURU	KURU
29	KURU	KURU	KURU	KURU	-----	KURU	4.90	KURU	4.79	2.38	KURU	KURU
30	KURU	KURU	KURU	KURU	-----	KURU	3.70	KURU	3.78	0.308	KURU	KURU
31	KURU	-----	KURU	KURU	-----	KURU	-----	KURU	-----	KURU	KURU	-----
Maks.	KURU	KURU	KURU	KURU	KURU	KURU	5.44	5.22	4.90	2.78	KURU	KURU
Min.	KURU	KURU	KURU	KURU	KURU	KURU	KURU	KURU	KURU	KURU	KURU	KURU
Ortalama	KURU	KURU	KURU	KURU	KURU	KURU	1.79	0.837	0.575	0.785	KURU	KURU
LT/SN/Km2	0.000	0.000	0.000	0.000	0.000	0.000	0.263	0.123	0.085	0.116	0.000	0.000
AKIM mm.	0.000	0.000	0.000	0.000	0.000	0.000	0.683	0.330	0.219	0.310	0.000	0.000
MİL. M3	0.000	0.000	0.000	0.000	0.000	0.000	4.64	2.24	1.49	2.10	0.000	0.000

SU YILI (2006) YILLIK TOPLAM AKIM 10.47 MİLYON M3 2 MM. 0.0 LT/SN/Km2

16. Konya Kapali Havzasi

D16A098 Melendiz Ç. Selime

YERİ : **AKSARAY GÜZELYURT SELİME BELDESİ.**
34°16'9" Doğu - 38°17'51" Kuzey

YAĞIŞ ALANI : **511,10 km2** **YAKLAŞIK KOT : 1129 m**

GÖZLEM SÜRESİ : **10.05.1973 - 30.09.2006**

ORTALAMA AKIMLAR : **Gözlem süresinde 2.131 m3/sn. (22 Yıllık) 2006 Su yılında 1.615 m3/sn.**

ANLIK EN ÇOK VE EN AZ AKIMLAR:

2006 Su yılında anlık encok akım	:	**7.60**	**m3/sn**	**02.04.2006**
2006 Su yılında anlık enaz akım	:	**0.614**	**m3/sn**	**17.07.2006**
Gözlem süresinde anlık encok akım	:	**31.0**	**m3/sn**	**06.06.1982**
Gözlem süresinde anlık enaz akım	:	**0.013**	**m3/sn**	**18.05.2000**

İstasyon için kullanılmış anahtar bulunamadı.

Akımlar 01 Ekim 2005 'den 30 Eylül 2006' a kadar m3/sn olarak

Gün	Ekim	Kasım	Aralık	Ocak	Şubat	Mart	Nisan	Mayıs	Haziran	Temmuz	Ağustos	Eylül
01	0.796	1.27	1.27	1.27	1.36	2.10	3.18	2.82	1.50	1.36	0.660	0.660
02	0.796	1.27	1.27	1.36	1.45	2.10	4.81	2.72	1.41	1.36	0.660	0.660
03	0.796	1.27	1.27	1.36	1.45	2.22	4.29	2.72	1.41	1.09	0.660	0.660
04	0.796	1.36	1.27	1.36	1.45	3.90	3.54	2.72	1.41	1.09	0.660	0.728
05	0.796	1.45	1.27	1.36	1.36	3.90	3.30	2.54	1.32	1.09	0.660	0.728
06	0.796	1.45	1.18	1.36	1.45	3.66	3.06	2.54	1.32	0.932	0.660	0.728
07	0.796	1.45	1.18	1.36	1.45	3.54	3.06	2.54	1.32	0.932	0.660	0.796
08	0.796	1.45	1.18	1.36	1.58	3.42	3.18	2.54	1.23	0.932	0.660	0.796
09	0.796	1.45	1.18	1.36	1.71	3.30	3.18	2.54	1.23	0.932	0.660	0.796
10	0.796	1.45	1.18	1.36	1.58	3.06	3.42	2.54	1.23	0.864	0.660	0.796
11	0.796	1.45	1.27	1.27	1.71	3.06	4.03	2.36	1.23	0.796	0.660	0.796
12	0.796	1.45	1.27	1.36	2.22	2.94	3.90	2.27	1.14	0.796	0.660	0.796
13	0.796	1.45	1.27	1.36	2.58	2.70	3.90	2.27	1.05	0.796	0.660	0.728
14	0.796	1.36	1.27	1.36	2.22	2.58	4.55	2.36	0.886	0.796	0.660	0.728
15	0.796	1.36	1.27	1.36	1.97	2.22	4.81	2.18	0.804	0.728	0.660	0.728
16	0.864	1.36	1.27	1.36	1.84	2.10	4.68	2.09	0.804	0.660	0.660	0.796
17	0.864	1.27	1.36	1.27	1.97	2.10	4.42	2.27	0.886	0.614	1.27	0.796
18	0.864	1.27	1.27	1.27	1.71	2.34	4.29	4.62	0.886	0.614	1.18	0.796
19	0.932	1.27	1.27	1.27	1.71	2.70	3.90	3.64	0.886	0.660	1.09	0.864
20	1.09	1.27	1.27	1.27	1.84	2.70	3.66	3.50	0.886	0.660	0.932	0.864
21	1.09	1.27	1.27	1.45	1.84	2.70	4.03	3.22	0.886	0.660	0.864	0.864
22	1.09	1.36	1.27	1.58	1.97	2.70	3.78	3.08	0.886	0.660	0.796	0.864
23	1.18	1.27	1.27	1.45	1.97	2.70	3.78	2.94	0.886	0.660	0.728	0.864
24	1.27	1.27	1.27	1.45	1.97	3.06	3.78	2.94	0.886	0.660	0.728	0.864
25	1.27	1.27	1.27	1.45	2.22	3.06	3.78	2.80	0.886	0.660	0.728	0.864
26	1.27	1.36	1.27	1.45	2.22	3.06	3.42	2.48	0.886	0.660	0.728	0.932
27	1.27	1.27	1.27	1.45	2.22	2.94	3.18	2.32	0.886	0.660	0.660	1.00
28	1.27	1.27	1.27	1.45	2.22	2.82	2.94	2.16	1.23	0.660	0.660	1.09
29	1.27	1.27	1.27	1.58	-----	2.70	2.70	1.80	1.70	0.660	0.660	1.09
30	1.27	1.27	1.27	1.45	-----	2.70	2.82	1.50	1.58	0.660	0.660	1.09
31	1.27	-----	1.27	1.27	-----	2.94	-----	1.50	-----	0.660	0.660	-----
Maks.	1.36	1.71	1.45	1.71	2.94	4.42	7.60	6.40	6.10	1.45	1.58	1.09
Min.	0.796	1.27	1.18	1.18	1.36	2.10	2.70	1.50	0.804	0.614	0.614	0.660
Ortalama	0.970	1.34	1.26	1.38	1.83	2.84	3.71	2.60	1.12	0.805	0.739	0.825
LT/SN/Km2	1.90	2.63	2.46	2.69	3.58	5.56	7.26	5.08	2.19	1.58	1.45	1.61
AKIM mm.	5.08	6.81	6.59	7.22	8.66	14.9	18.8	13.6	5.67	4.22	3.87	4.19
MİL. M3	2.60	3.48	3.37	3.69	4.43	7.60	9.62	6.96	2.90	2.16	1.98	2.14

SU YILI (2006) YILLIK TOPLAM AKIM 50.93 MİLYON M3 100 MM. 3.2 LT/SN/Km2

16. Konya Kapali Havzasi

D16A100 Meram Ç. Küçükmuhsine

YERİ : **KONYA BEYŞEHİR YOLUNDAN ALTIN APA BARAJINA VARMADAN SAĞA BAŞARIKAVAK YOLUNDAN 8 KM ULUMUHSINE KÖPRÜSÜNÜN 50 M MEMBASINDA**
32°16'7" Doğu - 37°55'24" Kuzey

YAĞIŞ ALANI : **401,70 km2** **YAKLAŞIK KOT : 1261 m**

GÖZLEM SÜRESİ : **01.01.1974 - 30.09.2006**

ORTALAMA AKIMLAR : **Gözlem süresinde 1.041 m3/sn. (26 Yıllık) 2006 Su yılında 0.656 m3/sn.**

ANLIK EN ÇOK VE EN AZ AKIMLAR:

2006 Su yılında anlık ençok akım	**:**	**16.2**	**m3/sn**	**24.04.2006**
2006 Su yılında anlık enaz akım	**:**	**0.001**	**m3/sn**	**10.08.2006**
Gözlem süresinde anlık ençok akım	**:**	**36.4**	**m3/sn**	**06.04.2003**
Gözlem süresinde anlık enaz akım	**:**	**0.000**	**m3/sn**	**16.10.1974**

İstasyon için kullanılmış anahtar bulunamadı.

Akımlar 01 Ekim 2005 'den 30 Eylül 2006' a kadar m3/sn olarak

Gün	Ekim	Kasım	Aralık	Ocak	Şubat	Mart	Nisan	Mayıs	Haziran	Temmuz	Ağustos	Eylül
01	0.350	0.290	0.683	0.500	0.683	1.53	1.53	1.82	0.425	0.220	0.025	0.011
02	0.350	0.290	0.683	0.500	0.683	1.41	1.53	1.82	0.350	0.170	0.025	0.025
03	0.350	0.290	0.683	0.500	0.683	1.41	1.53	1.82	0.350	0.170	0.025	0.025
04	0.350	0.290	0.592	0.500	0.683	1.41	1.41	1.82	0.350	0.170	0.045	0.025
05	0.350	0.290	0.500	0.500	0.592	1.41	1.41	2.65	0.290	0.220	0.011	0.025
06	0.350	0.290	0.500	0.500	0.683	1.41	1.29	2.16	0.290	0.220	0.011	0.025
07	0.350	0.350	0.500	0.500	0.592	1.29	1.17	1.82	0.220	0.220	0.025	0.025
08	0.350	0.350	0.500	0.500	0.683	1.17	1.41	1.82	0.220	0.170	0.025	0.025
09	0.350	0.350	0.500	0.500	0.683	1.17	1.29	2.33	0.220	0.170	0.011	0.025
10	0.290	0.290	0.500	0.500	0.775	1.05	1.29	1.82	0.220	0.170	0.005	0.025
11	0.290	0.290	0.500	0.500	0.775	1.05	1.29	1.65	0.290	0.170	0.005	0.025
12	0.290	0.290	0.500	0.500	0.775	1.05	1.17	1.41	0.290	0.170	0.011	0.045
13	0.290	0.290	0.500	0.500	0.958	1.17	1.17	1.29	0.350	0.170	0.005	0.025
14	0.290	0.290	0.500	0.500	0.958	1.17	1.17	1.29	0.350	0.170	0.011	0.025
15	0.350	0.290	0.500	0.500	0.867	1.17	1.17	1.17	0.290	0.170	0.011	0.025
16	0.425	0.290	0.500	0.500	0.775	1.17	1.53	1.17	0.220	0.170	0.005	0.025
17	0.350	0.290	0.500	0.500	0.775	1.17	1.29	1.17	0.220	0.120	0.005	0.025
18	0.290	0.290	0.500	0.500	0.775	1.41	1.17	1.05	0.220	0.120	0.005	0.025
19	0.290	0.290	0.500	0.500	0.958	1.65	1.05	1.05	0.170	0.120	0.425	0.025
20	0.290	0.350	0.425	0.500	1.05	1.82	0.867	0.867	0.170	0.120	0.078	0.025
21	0.290	0.775	0.425	0.500	1.29	1.65	0.867	0.775	0.170	0.120	0.045	0.025
22	0.290	0.683	0.425	0.500	1.41	1.65	0.958	0.683	0.170	0.120	0.025	0.120
23	0.290	0.683	0.500	0.500	1.53	1.65	1.17	0.592	0.170	0.120	0.025	0.220
24	0.290	0.683	0.500	0.500	1.53	1.82	10.0	0.592	0.170	0.120	0.025	0.350
25	0.290	0.683	0.500	0.500	1.53	1.82	6.00	0.500	0.170	0.078	0.025	0.290
26	0.290	0.683	0.500	0.592	1.65	1.65	3.70	0.500	0.170	0.045	0.025	0.290
27	0.290	0.683	0.500	0.683	1.65	1.65	2.95	1.05	0.170	0.045	0.025	0.220
28	0.290	0.775	0.500	0.683	1.65	1.53	2.65	0.775	0.170	0.045	0.025	0.220
29	0.290	0.775	0.500	0.683	-----	1.41	2.33	0.592	0.170	0.045	0.025	0.220
30	0.290	0.775	0.500	0.683	-----	1.41	1.99	0.500	0.220	0.045	0.025	0.220
31	0.290	-----	0.500	0.683	-----	1.53	-----	0.500	-----	0.045	0.011	-----
Maks.	0.425	0.958	0.775	0.683	1.65	1.99	16.2	3.40	0.500	0.290	1.53	0.958
Min.	0.290	0.290	0.425	0.500	0.592	1.05	0.867	0.500	0.170	0.045	0.001	0.011
Ortalama	0.316	0.441	0.513	0.532	0.987	1.41	1.95	1.26	0.242	0.136	0.034	0.089
LT/SN/Km2	0.786	1.10	1.28	1.33	2.46	3.52	4.84	3.14	0.602	0.340	0.084	0.222
AKIM mm.	2.10	2.85	3.42	3.55	5.95	9.43	12.6	8.40	1.56	0.909	0.226	0.577
MİL. M3	0.845	1.14	1.38	1.43	2.39	3.79	5.04	3.37	0.627	0.365	0.091	0.232

SU YILI (2006) YILLIK TOPLAM AKIM 20.70 MİLYON M3 52 MM. 1.6 LT/SN/Km2

16. Konya Kapali Havzasi

D16A101 Çavus D. Asagiesence

YERİ : **SEYDİŞEHİR A.ESENCE BELDESİ.**
31°50'53" Doğu - 37°35'25" Kuzey

YAĞIŞ ALANI : **376,80 km2** **YAKLAŞIK KOT : 1111 m**

GÖZLEM SÜRESİ : **14.11.1973 - 30.09.2006**

ORTALAMA AKIMLAR : **Gözlem süresinde 0.953 m3/sn. (29 Yıllık) 2006 Su yılında 0.593 m3/sn.**

ANLIK EN ÇOK VE EN AZ AKIMLAR:

2006 Su yılında anlık ençok akım	**:**	**13.4**	**m3/sn**	**13.03.2006**
2006 Su yılında anlık enaz akım	**:**	**0.000**	**m3/sn**	**01.10.2005**
Gözlem süresinde anlık ençok akım	**:**	**216.**	**m3/sn**	**26.12.2001**
Gözlem süresinde anlık enaz akım	**:**	**0.000**	**m3/sn**	**01.10.1974**

İstasyon için kullanılmış anahtar bulunamadı.

Akımlar 01 Ekim 2005 'den 30 Eylül 2006' a kadar m3/sn olarak

Gün	Ekim	Kasım	Aralık	Ocak	Şubat	Mart	Nisan	Mayıs	Haziran	Temmuz	Ağustos	Eylül
01	KURU	0.170	0.390	0.390	0.280	1.82	2.06	0.475	0.042	0.096	0.096	KURU
02	KURU	0.170	0.390	0.390	0.280	1.58	2.06	0.475	0.042	0.096	0.096	KURU
03	KURU	0.280	0.390	0.390	0.280	1.34	1.82	0.475	0.042	0.096	0.096	0.096
04	KURU	0.170	0.390	0.390	0.390	1.34	1.58	0.767	0.042	0.170	0.096	0.170
05	KURU	0.280	0.280	0.390	0.390	1.10	1.34	1.34	0.010	0.096	0.096	0.170
06	KURU	0.280	0.280	0.390	0.390	1.10	1.10	0.631	0.010	0.096	0.096	0.170
07	KURU	0.390	0.280	0.500	2.34	0.933	1.10	0.631	0.010	0.096	0.042	0.096
08	KURU	0.631	0.280	0.930	2.64	1.10	1.10	0.500	0.010	0.096	0.042	0.096
09	KURU	0.500	0.280	0.794	1.55	1.10	1.10	0.500	0.010	0.096	0.042	0.170
10	KURU	0.500	0.280	0.631	1.80	0.767	1.10	0.390	0.010	0.096	0.042	0.096
11	KURU	0.500	0.280	0.500	3.28	0.767	1.10	0.280	KURU	0.096	0.010	0.096
12	KURU	0.500	0.280	0.500	3.80	0.767	0.933	0.280	0.010	0.096	0.010	0.096
13	KURU	0.500	0.280	0.390	3.50	3.80	0.767	0.170	0.010	0.096	KURU	0.042
14	KURU	0.500	0.280	0.390	2.30	6.10	0.767	0.170	0.010	0.096	0.010	0.096
15	KURU	0.500	0.280	0.500	1.82	6.68	0.767	0.096	0.010	0.096	0.042	0.096
16	KURU	0.500	0.280	0.500	0.933	3.80	1.10	0.096	0.010	0.042	0.042	0.096
17	0.010	0.500	0.280	0.500	0.933	3.20	0.767	0.096	0.010	0.096	0.010	0.096
18	0.042	0.500	0.280	0.390	0.933	3.80	0.600	0.096	0.010	0.096	0.280	0.010
19	0.096	0.500	0.500	0.500	2.06	3.80	0.475	0.096	0.096	0.042	0.631	KURU
20	0.096	0.500	0.500	1.34	2.60	3.20	0.350	0.096	0.096	KURU	0.170	KURU
21	0.096	0.500	0.390	0.930	3.20	2.90	0.250	0.096	0.096	0.010	0.170	KURU
22	0.096	0.390	0.390	0.794	2.60	2.90	0.350	0.096	0.096	0.042	0.096	KURU
23	0.096	0.390	0.390	0.631	2.60	2.90	0.600	0.096	0.042	0.042	0.010	KURU
24	0.096	0.390	0.280	0.500	2.30	3.20	2.60	0.096	0.042	0.280	KURU	KURU
25	0.096	0.390	0.280	0.390	2.30	2.60	1.34	0.096	0.096	0.170	KURU	KURU
26	0.096	0.390	0.390	0.390	2.30	2.30	0.933	0.096	0.042	0.170	0.042	KURU
27	0.096	0.390	0.390	0.390	2.30	2.30	0.600	0.096	0.042	0.096	0.042	KURU
28	0.096	0.390	0.390	0.390	2.06	2.60	0.600	0.042	0.042	0.096	0.010	KURU
29	0.096	0.390	0.390	0.500	-----	2.06	0.600	0.042	0.042	0.170	KURU	KURU
30	0.096	0.390	0.390	0.390	-----	2.06	0.600	0.042	0.096	0.170	KURU	KURU
31	0.170	-----	0.390	0.390	-----	2.30	-----	0.042	-----	0.096	KURU	-----
Maks.	0.170	0.794	0.631	1.55	6.06	13.4	5.18	2.90	0.631	0.631	4.71	0.390
Min.	KURU	0.096	0.170	0.390	0.035	0.767	0.250	0.042	KURU	KURU	KURU	KURU
Ortalama	0.044	0.413	0.340	0.529	1.86	2.46	1.02	0.274	0.038	0.101	0.075	0.056
LT/SN/Km2	0.118	1.10	0.903	1.40	4.94	6.52	2.69	0.728	0.100	0.268	0.199	0.150
AKIM mm.	0.315	2.84	2.42	3.76	12.0	17.5	6.98	1.95	0.258	0.718	0.532	0.388
MİL. M3	0.119	1.07	0.912	1.42	4.51	6.58	2.63	0.734	0.097	0.271	0.200	0.146

SU YILI (2006) YILLIK TOPLAM AKIM 18.69 MİLYON M3 50 MM. 1.6 LT/SN/Km2

16. Konya Kapali Havzasi

D16A104 Sarisu Eyikler

YERİ : **BEYŞEHİR**
31°42'59" Doğu - 37°42'57" Kuzey

YAĞIŞ ALANI : **1040,00 km2** **YAKLAŞIK KOT : 1140 m**

GÖZLEM SÜRESİ : **01.10.1991 - 30.09.2006**

ORTALAMA AKIMLAR : **Gözlem süresinde 2.664 m3/sn. (20 Yıllık) 2006 Su yılında 1.192 m3/sn.**

ANLIK EN ÇOK VE EN AZ AKIMLAR:

2006 Su yılında anlık ençok akım	**:**	**9.28**	**m3/sn**	**25.04.2006**
2006 Su yılında anlık enaz akım	**:**	**0.068**	**m3/sn**	**17.08.2006**
Gözlem süresinde anlık ençok akım	**:**	**48.0**	**m3/sn**	**16.01.1979**
Gözlem süresinde anlık enaz akım	**:**	**0.000**	**m3/sn**	**01.10.1974**

İstasyon için kullanılmış anahtar bulunamadı.

Akımlar 01 Ekim 2005 'den 30 Eylül 2006' a kadar m3/sn olarak

Gün	Ekim	Kasım	Aralık	Ocak	Şubat	Mart	Nisan	Mayıs	Haziran	Temmuz	Ağustos	Eylül
01	0.694	0.860	1.20	0.740	0.740	2.50	3.36	1.70	0.220	0.140	0.270	0.100
02	0.588	0.600	1.20	0.740	0.740	2.30	3.36	1.70	0.260	0.180	0.270	0.205
03	0.694	0.740	1.20	0.600	0.740	2.30	3.36	1.90	0.260	0.220	0.270	0.376
04	0.694	0.740	1.20	0.600	0.600	2.30	3.36	1.70	0.220	0.220	0.205	0.376
05	0.694	0.860	1.03	0.600	0.740	2.50	3.36	2.10	0.180	0.220	0.140	0.270
06	0.694	0.860	1.03	0.740	0.860	2.30	3.36	2.10	0.180	0.140	0.140	0.270
07	0.588	0.860	1.03	0.740	1.03	2.30	3.14	1.70	0.180	0.140	0.140	0.270
08	0.588	1.03	1.03	0.740	1.36	2.30	3.14	1.53	0.180	0.100	0.140	0.270
09	0.482	1.03	1.03	0.740	1.53	2.30	3.14	2.10	0.220	0.100	0.140	0.270
10	0.482	1.20	0.860	0.740	1.53	2.30	3.14	2.30	0.300	0.100	0.140	0.270
11	0.694	1.20	0.860	0.740	1.70	2.30	2.70	2.10	0.380	0.100	0.100	0.205
12	0.694	1.03	0.860	0.740	2.92	2.30	2.70	2.50	0.380	0.100	0.100	0.205
13	0.694	1.20	0.860	0.740	4.52	2.50	2.70	2.70	0.490	0.070	0.100	0.205
14	0.800	1.20	0.860	0.740	3.14	3.14	2.50	2.10	0.490	0.070	0.100	0.205
15	0.694	1.20	0.860	0.740	2.50	4.76	2.50	2.10	0.490	0.376	0.100	0.270
16	0.800	1.20	0.860	0.740	1.70	6.98	2.50	2.10	0.490	0.270	0.100	0.205
17	0.940	1.20	0.860	0.740	1.53	5.66	2.50	2.30	0.490	0.205	0.100	0.205
18	0.800	1.20	0.860	0.740	1.70	4.28	2.30	1.90	0.490	0.270	0.100	0.205
19	1.36	1.36	0.860	0.740	1.70	4.76	2.30	2.30	0.300	0.205	0.100	0.376
20	1.08	1.36	0.740	0.740	2.30	5.66	2.10	1.90	0.260	0.270	0.100	0.270
21	1.08	1.70	0.740	0.740	3.36	4.52	2.10	1.70	0.260	0.270	0.694	0.205
22	1.08	1.53	0.600	0.740	3.36	3.80	1.90	1.70	0.220	0.270	0.205	0.482
23	1.08	1.36	0.740	0.740	2.92	3.58	2.10	1.20	0.220	0.205	0.100	0.482
24	1.08	1.36	0.600	0.740	2.70	3.36	4.76	0.860	0.180	0.205	0.100	0.482
25	0.800	1.36	0.600	0.740	2.70	3.58	6.54	0.600	0.140	0.270	0.100	0.482
26	1.08	1.36	0.600	0.740	2.50	3.36	4.04	0.300	0.070	0.270	0.100	0.588
27	1.08	1.36	0.600	0.740	2.30	3.36	2.70	0.300	0.100	0.140	0.100	0.588
28	0.800	1.36	0.600	0.740	2.70	3.36	2.10	0.300	0.140	0.205	0.100	0.694
29	0.694	1.36	0.600	0.740	-----	3.36	2.10	0.260	0.140	0.205	0.100	0.482
30	1.08	1.20	0.740	0.740	-----	3.36	1.70	0.220	0.180	0.205	0.100	0.482
31	1.08	-----	0.740	0.740	-----	3.36	-----	0.260	-----	0.270	0.100	-----
Maks.	4.67	1.70	1.20	0.740	4.76	9.02	9.28	6.32	0.600	0.376	1.08	1.08
Min.	0.100	0.380	0.600	0.600	0.600	1.70	1.70	0.220	0.070	0.070	0.068	0.068
Ortalama	0.829	1.16	0.853	0.726	2.00	3.38	2.92	1.57	0.270	0.194	0.150	0.333
LT/SN/Km2	0.797	1.12	0.820	0.699	1.93	3.25	2.81	1.51	0.260	0.186	0.144	0.320
AKIM mm.	2.13	2.90	2.20	1.87	4.66	8.70	7.27	4.03	0.674	0.499	0.387	0.830
MİL. M3	2.22	3.01	2.29	1.95	4.85	9.05	7.57	4.19	0.701	0.519	0.402	0.864

SU YILI (2006) YILLIK TOPLAM AKIM 37.62 MİLYON M3 36 MM. 1.1 LT/SN/Km2

16. Konya Kapali Havzasi

D16A109 Çavuscu G. Çikis (Orhaniye)

YERİ : **ILGIN ORHANİYE KÖYÜ.**
31°58'54" Doğu - 38°17'24" Kuzey

YAĞIŞ ALANI : **---- km2** **YAKLAŞIK KOT : 1030 m**

GÖZLEM SÜRESİ : **01.07.1973 - 30.09.2006**

ORTALAMA AKIMLAR : **Gözlem süresinde 1.827 m3/sn. (27 Yıllık) 2006 Su yılında 0.619 m3/sn.**

ANLIK EN ÇOK VE EN AZ AKIMLAR:

2006 Su yılında anlık ençok akım	:	**7.20**	**m3/sn**	**28.04.2006**
2006 Su yılında anlık enaz akım	:	**0.000**	**m3/sn**	**01.10.2005**
Gözlem süresinde anlık ençok akım	:	**17.4**	**m3/sn**	**29.04.1977**
Gözlem süresinde anlık enaz akım	:	**0.000**	**m3/sn**	**01.10.1993**

İstasyon için kullanılmış anahtar bulunamadı.

Akımlar 01 Ekim 2005 'den 30 Eylül 2006' a kadar m3/sn olarak

Gün	Ekim	Kasım	Aralık	Ocak	Şubat	Mart	Nisan	Mayıs	Haziran	Temmuz	Ağustos	Eylül
01	KURU	KURU	KURU	0.060	0.060	0.120	0.070	5.70	0.350	2.10	0.060	0.060
02	KURU	KURU	KURU	0.060	0.060	0.120	0.070	5.70	0.120	2.90	0.060	0.027
03	KURU	KURU	KURU	0.040	0.060	0.090	0.070	5.60	0.090	2.80	0.060	0.003
04	KURU	KURU	KURU	0.040	0.060	0.090	0.070	5.50	0.170	2.80	0.060	KURU
05	KURU	KURU	KURU	0.040	0.060	0.090	0.060	5.30	0.170	2.80	0.060	KURU
06	KURU	KURU	KURU	0.040	0.060	0.090	0.060	5.20	0.140	2.70	0.060	KURU
07	KURU	KURU	KURU	0.040	0.060	0.090	0.060	5.20	0.140	2.50	0.060	KURU
08	KURU	KURU	KURU	0.040	0.060	0.090	0.060	5.10	0.190	0.850	0.060	KURU
09	KURU	KURU	0.006	0.040	0.060	0.070	0.060	5.30	0.140	0.120	0.060	KURU
10	KURU	KURU	0.017	0.040	0.060	0.070	0.060	5.10	0.140	0.120	0.060	KURU
11	KURU	KURU	0.017	0.040	0.060	0.070	0.060	5.20	0.140	0.120	0.060	KURU
12	KURU	KURU	0.017	0.040	0.060	0.070	0.060	5.40	0.140	0.190	0.070	KURU
13	KURU	KURU	0.017	0.040	0.070	0.070	0.060	5.50	0.140	0.230	0.060	KURU
14	KURU	KURU	0.017	0.040	0.070	0.070	0.060	5.40	0.140	0.140	0.060	KURU
15	KURU	KURU	0.017	0.040	0.070	0.070	0.060	5.30	0.140	0.090	0.060	KURU
16	KURU	KURU	0.017	0.040	0.070	0.070	0.060	5.40	0.170	0.090	0.060	KURU
17	KURU	KURU	0.017	0.040	0.070	0.070	0.060	5.40	0.140	0.090	0.060	KURU
18	KURU	KURU	0.017	0.040	0.090	0.070	0.060	5.30	0.190	0.090	0.060	KURU
19	KURU	KURU	0.040	0.040	0.090	0.070	0.060	5.30	0.140	0.090	0.060	KURU
20	KURU	KURU	0.027	0.040	0.090	0.070	1.05	5.20	0.120	0.090	0.060	KURU
21	KURU	KURU	0.027	0.060	0.090	0.090	2.10	5.20	0.120	0.090	0.060	KURU
22	KURU	KURU	0.040	0.060	0.120	0.090	3.10	5.20	0.140	0.070	0.060	KURU
23	KURU	KURU	0.040	0.060	0.120	0.090	3.70	5.20	0.140	0.070	0.060	KURU
24	KURU	KURU	0.040	0.060	0.120	0.090	3.60	5.20	0.120	0.070	0.060	KURU
25	KURU	KURU	0.040	0.060	0.120	0.090	0.460	5.10	0.120	0.070	0.060	KURU
26	KURU	KURU	0.040	0.060	0.120	0.090	0.190	4.70	0.120	0.060	0.060	KURU
27	KURU	KURU	0.040	0.060	0.120	0.090	0.140	3.30	0.120	0.060	0.060	KURU
28	KURU	KURU	0.060	0.060	0.120	0.090	4.60	4.70	0.120	0.060	0.060	KURU
29	KURU	KURU	0.060	0.060	-----	0.070	5.20	4.60	0.170	0.060	0.060	KURU
30	KURU	KURU	0.060	0.060	-----	0.070	5.60	4.60	0.900	0.060	0.060	KURU
31	KURU	-----	0.060	0.060	-----	0.070	-----	4.30	-----	0.060	0.060	-----
Maks.	KURU	KURU	0.060	0.070	0.120	0.120	7.20	6.00	3.00	3.10	0.190	0.060
Min.	KURU	KURU	KURU	0.040	0.060	0.070	0.060	0.540	0.090	0.060	0.060	KURU
Ortalama	KURU	KURU	0.024	0.048	0.081	0.082	1.03	5.14	0.173	0.698	0.060	0.003
LT/SN/Km2	0.000	0.000	0.000	0.000	0.000	0.000	0.000	0.000	0.000	0.000	0.000	0.000
AKIM mm.	0.000	0.000	0.000	0.000	0.000	0.000	0.000	0.000	0.000	0.000	0.000	0.000
MİL. M3	0.000	0.000	0.063	0.130	0.196	0.220	2.67	13.8	0.448	1.87	0.162	0.008

SU YILI (2006) YILLIK TOPLAM AKIM 19.57 MİLYON M3 0 MM. 0.0 LT/SN/Km2

16. Konya Kapali Havzasi

D16A111 Soguksu Yesildag Köp.

YERİ : **İstasyona Ait Adres Bilgisi Girilmemiştir.**
31°39'0" Doğu - 37°32'0" Kuzey

YAĞIŞ ALANI : **42,00 km2** **YAKLAŞIK KOT : 1124 m**

GÖZLEM SÜRESİ : **01.10.1976 - 30.09.2006**

ORTALAMA AKIMLAR : **Gözlem süresinde 3.824 m3/sn. (12 Yıllık) 2006 Su yılında 3.980 m3/sn.**

ANLIK EN ÇOK VE EN AZ AKIMLAR:

2006 Su yılında anlık ençok akım	**:**	**59.4**	**m3/sn**	**12.02.2006**
2006 Su yılında anlık enaz akım	**:**	**0.195**	**m3/sn**	**05.10.2005**
Gözlem süresinde anlık ençok akım	**:**	**59.4**	**m3/sn**	**12.02.2006**
Gözlem süresinde anlık enaz akım	**:**	**0.000**	**m3/sn**	**01.02.1995**

İstasyon için kullanılmış anahtar bulunamadı.

Akımlar 01 Ekim 2005 'den 30 Eylül 2006' a kadar m3/sn olarak

Gün	Ekim	Kasım	Aralık	Ocak	Şubat	Mart	Nisan	Mayıs	Haziran	Temmuz	Ağustos	Eylül
01	0.195	0.195	1.75	1.90	1.75	10.7	11.2	6.42	3.38	1.45	0.706	0.424
02	0.195	0.195	1.75	1.90	1.75	10.7	10.7	6.42	3.38	1.19	0.612	0.354
03	0.195	0.195	1.60	1.75	1.75	10.7	10.3	6.42	3.14	1.06	0.612	0.354
04	0.195	0.195	1.45	1.75	1.75	13.6	10.3	6.42	3.14	1.06	0.612	0.354
05	0.195	0.195	1.32	1.75	1.90	12.1	9.96	6.42	3.14	1.06	0.612	0.354
06	0.195	0.195	1.32	2.05	2.80	11.2	9.96	6.42	3.14	1.06	0.612	0.354
07	0.195	0.195	1.19	2.40	3.77	10.7	9.96	6.42	2.90	1.06	0.612	0.354
08	0.195	0.230	1.06	2.40	3.96	10.7	10.3	6.71	2.70	1.06	0.612	0.354
09	0.195	0.270	1.06	2.40	3.96	10.7	9.96	6.42	2.70	1.06	0.612	0.354
10	0.195	0.310	0.930	2.40	12.5	10.3	9.59	6.13	2.70	1.06	0.612	0.354
11	0.195	0.310	0.930	2.20	21.8	9.59	8.85	6.13	2.50	0.930	0.612	0.354
12	0.195	0.356	0.930	2.05	59.4	9.22	9.22	5.84	2.50	0.930	0.612	0.354
13	0.195	0.356	0.930	2.05	50.9	9.22	9.59	5.84	2.50	0.930	0.612	0.354
14	0.195	0.356	0.930	1.90	32.7	15.0	9.59	5.84	2.50	0.930	0.612	0.354
15	0.195	0.356	0.800	1.75	16.0	16.0	9.96	5.55	2.50	0.930	0.612	0.354
16	0.195	0.356	0.800	1.75	11.7	13.1	10.3	5.26	2.50	0.930	0.612	0.354
17	0.195	0.356	0.930	1.60	9.96	12.1	11.2	5.26	2.50	0.930	0.612	0.354
18	0.195	0.796	4.72	1.60	8.48	11.7	9.96	4.97	2.50	0.930	0.612	0.354
19	0.195	3.39	7.00	1.60	8.11	11.7	8.85	4.97	1.60	0.930	0.612	0.354
20	0.195	5.67	6.05	1.75	7.74	11.2	8.85	4.97	1.60	0.930	0.612	0.354
21	0.230	5.67	5.86	1.90	7.37	10.7	8.85	4.68	1.60	0.930	0.612	0.354
22	0.230	4.53	5.86	1.90	7.74	10.3	8.11	4.39	1.60	0.930	0.612	0.354
23	0.230	3.96	6.81	2.05	8.11	10.3	7.37	4.39	1.60	0.930	0.612	0.354
24	0.230	3.39	6.43	2.20	8.48	10.7	8.11	4.39	1.60	0.930	0.612	0.354
25	0.230	2.80	6.05	2.20	8.85	12.1	8.11	4.39	1.60	0.930	0.612	0.354
26	0.230	2.40	5.86	2.05	9.22	11.2	7.37	4.10	1.60	0.930	0.612	0.354
27	0.230	2.20	5.48	2.05	9.96	11.2	7.00	4.10	1.60	0.800	0.612	0.354
28	0.230	2.20	2.80	2.05	10.7	10.7	7.00	3.86	1.45	0.800	0.612	0.354
29	0.230	2.20	2.20	1.90	-----	10.7	7.00	3.62	1.45	0.800	0.612	0.354
30	0.230	2.05	2.20	1.90	-----	10.7	7.00	3.38	1.45	0.706	0.612	0.354
31	0.195	-----	2.05	1.90	-----	11.7	-----	3.38	-----	0.706	0.518	-----
Maks.	0.270	6.24	7.18	2.40	59.4	23.5	12.6	7.37	3.38	1.60	0.706	0.612
Min.	0.195	0.195	0.612	1.32	1.60	9.22	7.00	3.38	1.45	0.612	0.424	0.330
Ortalama	0.206	1.53	2.87	1.97	11.9	11.3	9.15	5.27	2.30	0.962	0.612	0.356
LT/SN/Km2	4.91	36.4	68.4	46.9	283.	269.	218.	126.	54.8	22.9	14.6	8.48
AKIM mm.	13.2	94.4	183.	126.	685.	721.	565.	336.	142.	61.3	39.0	22.0
MİL. M3	0.553	3.96	7.69	5.27	28.8	30.3	23.7	14.1	5.97	2.58	1.64	0.924

SU YILI (2006) YILLIK TOPLAM AKIM 125.49 MİLYON M3 2988 MM. 94.8 LT/SN/Km2

16. Konya Kapali Havzasi

D16A115 Çarsamba S. Sorkun

YERİ : **BOZKIR SORKUN.**
32°8'58" Doğu - 37°9'56" Kuzey

YAĞIŞ ALANI : **84,00 km2** **YAKLAŞIK KOT : 1150 m**

GÖZLEM SÜRESİ : **01.12.1976 - 30.09.2006**

ORTALAMA AKIMLAR : **Gözlem süresinde 2.366 m3/sn. (28 Yıllık) 2006 Su yılında 1.759 m3/sn.**

ANLIK EN ÇOK VE EN AZ AKIMLAR:

2006 Su yılında anlık ençok akım	**:**	**10.5**	**m3/sn**	**16.04.2006**
2006 Su yılında anlık enaz akım	**:**	**0.270**	**m3/sn**	**11.10.2005**
Gözlem süresinde anlık ençok akım	**:**	**38.7**	**m3/sn**	**05.03.2004**
Gözlem süresinde anlık enaz akım	**:**	**0.000**	**m3/sn**	**01.12.1980**

İstasyon için kullanılmış anahtar bulunamadı.

Akımlar 01 Ekim 2005 'den 30 Eylül 2006' a kadar m3/sn olarak

Gün	Ekim	Kasım	Aralık	Ocak	Şubat	Mart	Nisan	Mayıs	Haziran	Temmuz	Ağustos	Eylül
01	0.398	0.334	0.910	0.846	1.17	2.92	7.24	4.60	1.68	0.846	0.462	0.270
02	0.398	0.334	0.910	0.846	1.17	3.16	7.90	4.36	1.68	0.782	0.462	0.270
03	0.398	0.334	0.782	0.846	1.17	3.64	7.24	4.36	1.68	0.782	0.462	0.270
04	0.334	0.334	0.782	0.846	1.17	4.60	6.91	4.36	1.68	0.782	0.462	0.270
05	0.334	0.334	0.782	0.846	1.17	4.36	6.25	3.88	1.68	0.782	0.462	0.270
06	0.334	0.334	0.782	0.846	1.30	4.12	6.25	3.88	1.68	0.782	0.398	0.270
07	0.334	0.398	0.782	0.846	1.94	3.88	6.25	3.88	1.56	0.782	0.398	0.270
08	0.334	0.398	0.782	0.910	1.81	3.88	6.25	3.88	1.56	0.782	0.334	0.270
09	0.334	0.398	0.718	0.910	1.56	3.64	6.25	3.64	1.56	0.654	0.334	0.270
10	0.270	0.398	0.718	0.910	1.56	3.16	6.25	3.64	1.56	0.654	0.334	0.270
11	0.270	0.462	0.718	0.910	1.94	2.68	6.25	3.64	1.56	0.590	0.334	0.270
12	0.270	0.462	0.718	0.910	2.44	2.68	6.25	3.40	1.43	0.590	0.334	0.270
13	0.334	0.526	0.654	0.910	2.44	3.16	6.25	3.40	1.30	0.590	0.334	0.270
14	0.334	0.590	0.654	0.910	2.07	3.40	6.25	3.40	1.30	0.590	0.334	0.270
15	0.334	0.590	0.654	0.910	1.81	3.40	6.58	3.40	1.30	0.590	0.334	0.270
16	0.334	0.590	0.654	0.910	1.81	3.40	9.72	3.40	1.17	0.590	0.334	0.270
17	0.334	0.590	0.654	0.910	1.68	3.16	8.68	3.40	1.04	0.590	0.334	0.270
18	0.334	0.718	0.654	0.910	1.56	3.16	8.16	3.40	1.04	0.590	0.334	0.270
19	0.334	1.04	0.910	0.910	1.56	3.16	7.57	3.40	1.04	0.590	0.334	0.270
20	0.334	1.17	1.30	1.68	1.56	3.40	7.24	3.16	1.04	0.590	0.334	0.270
21	0.334	1.43	1.04	1.43	1.68	3.40	6.91	3.16	1.04	0.590	0.334	0.270
22	0.334	1.17	0.910	1.43	1.68	3.88	6.91	2.92	1.04	0.590	0.270	0.334
23	0.334	0.846	0.910	1.43	1.81	4.60	6.58	2.44	1.04	0.526	0.270	0.334
24	0.334	0.846	0.910	1.43	1.94	6.25	6.25	2.44	1.04	0.462	0.270	0.334
25	0.334	0.782	0.910	1.43	2.07	6.91	6.25	2.20	1.04	0.462	0.270	0.334
26	0.334	0.718	0.846	1.43	2.44	6.25	5.26	2.20	0.910	0.462	0.270	0.334
27	0.334	0.718	0.846	1.43	2.68	5.92	4.93	2.20	0.846	0.462	0.270	0.334
28	0.334	0.718	0.846	1.30	2.92	5.92	4.60	2.20	0.846	0.462	0.270	0.334
29	0.334	0.782	0.846	1.17	-----	5.92	4.60	2.07	0.846	0.462	0.270	0.334
30	0.334	0.846	0.846	1.17	-----	6.25	4.60	1.68	0.846	0.462	0.270	0.270
31	0.334	-----	0.846	1.17	-----	7.24	-----	1.68	-----	0.462	0.270	-----
Maks.	0.398	1.43	1.30	1.81	3.16	7.90	10.5	4.60	1.68	0.846	0.462	0.334
Min.	0.270	0.270	0.654	0.846	1.17	2.68	4.60	1.68	0.846	0.398	0.270	0.270
Ortalama	0.334	0.640	0.815	1.08	1.79	4.24	6.55	3.22	1.27	0.611	0.338	0.287
LT/SN/Km2	3.98	7.62	9.71	12.8	21.3	50.5	78.0	38.3	15.1	7.27	4.03	3.42
AKIM mm.	10.6	19.7	26.0	34.3	51.5	135.	202.	103.	39.1	19.5	10.8	8.86
MİL. M3	0.895	1.66	2.18	2.88	4.33	11.4	17.0	8.61	3.29	1.64	0.906	0.744

SU YILI (2006) YILLIK TOPLAM AKIM 55.54 MİLYON M3 661 MM. 20.9 LT/SN/Km2

16. Konya Kapali Havzasi

D16A117 Seyithasan D. Seyithasan

YERİ : **KARAMAN SEYİTHASAN KÖYÜ.**
33°13'18" Doğu - 37°4'14" Kuzey

YAĞIŞ ALANI : **124,40 km2** **YAKLAŞIK KOT : 1140 m**

GÖZLEM SÜRESİ : **12.04.1978 - 30.09.2006**

ORTALAMA AKIMLAR : **Gözlem süresinde 0.443 m3/sn. (27 Yıllık) 2006 Su yılında 0.134 m3/sn.**

ANLIK EN ÇOK VE EN AZ AKIMLAR:

2006 Su yılında anlık ençok akım	**:**	**5.20**	**m3/sn**	**14.03.2006**
2006 Su yılında anlık enaz akım	**:**	**0.000**	**m3/sn**	**01.10.2005**
Gözlem süresinde anlık ençok akım	**:**	**120.**	**m3/sn**	**27.12.1981**
Gözlem süresinde anlık enaz akım	**:**	**0.000**	**m3/sn**	**11.01.1978**

İstasyon için kullanılmış anahtar bulunamadı.

Akımlar 01 Ekim 2005 'den 30 Eylül 2006' a kadar m3/sn olarak

Gün	Ekim	Kasım	Aralık	Ocak	Şubat	Mart	Nisan	Mayıs	Haziran	Temmuz	Ağustos	Eylül
01	KURU	KURU	KURU	KURU	KURU	0.710	0.325	0.121	KURU	KURU	KURU	KURU
02	KURU	KURU	KURU	KURU	KURU	0.601	1.20	0.121	KURU	KURU	KURU	KURU
03	KURU	KURU	KURU	KURU	KURU	0.601	0.601	0.121	KURU	KURU	KURU	KURU
04	KURU	KURU	KURU	KURU	KURU	0.601	0.408	0.121	KURU	KURU	KURU	KURU
05	KURU	KURU	KURU	KURU	KURU	0.601	0.325	0.121	KURU	KURU	KURU	KURU
06	KURU	KURU	KURU	KURU	KURU	0.601	0.243	0.121	KURU	KURU	KURU	KURU
07	KURU	KURU	KURU	KURU	0.179	0.601	0.243	0.121	KURU	KURU	KURU	KURU
08	KURU	KURU	KURU	KURU	0.601	0.601	0.243	0.045	KURU	KURU	KURU	KURU
09	KURU	KURU	KURU	KURU	0.408	0.601	0.179	0.045	KURU	KURU	KURU	KURU
10	KURU	KURU	KURU	KURU	0.408	0.601	0.179	0.045	KURU	KURU	KURU	KURU
11	KURU	KURU	KURU	KURU	0.601	0.601	0.121	0.045	KURU	KURU	KURU	KURU
12	KURU	KURU	KURU	KURU	0.601	0.408	0.121	0.045	KURU	KURU	KURU	KURU
13	KURU	KURU	KURU	KURU	0.870	0.601	0.121	0.045	KURU	KURU	KURU	KURU
14	KURU	KURU	KURU	KURU	0.710	2.60	0.121	0.045	KURU	KURU	KURU	KURU
15	KURU	KURU	KURU	KURU	0.601	2.60	0.121	0.045	KURU	KURU	KURU	KURU
16	KURU	KURU	KURU	KURU	0.601	1.75	0.121	0.045	KURU	KURU	KURU	KURU
17	KURU	KURU	KURU	KURU	0.601	1.65	0.121	0.045	KURU	KURU	KURU	KURU
18	KURU	KURU	KURU	KURU	0.601	1.65	0.121	0.045	KURU	KURU	KURU	KURU
19	KURU	KURU	KURU	KURU	0.601	1.20	0.121	0.045	KURU	KURU	KURU	KURU
20	KURU	KURU	KURU	KURU	0.601	0.870	0.121	0.045	KURU	KURU	KURU	KURU
21	KURU	KURU	KURU	KURU	0.601	0.870	0.121	0.045	KURU	KURU	KURU	KURU
22	KURU	KURU	KURU	KURU	0.601	0.870	0.121	0.019	KURU	KURU	KURU	KURU
23	KURU	KURU	KURU	KURU	0.601	0.710	0.121	0.019	KURU	KURU	KURU	KURU
24	KURU	KURU	KURU	KURU	0.601	0.601	0.121	KURU	KURU	KURU	KURU	KURU
25	KURU	KURU	KURU	KURU	0.601	0.601	0.503	KURU	KURU	KURU	KURU	KURU
26	KURU	KURU	KURU	KURU	0.601	0.601	0.503	KURU	KURU	KURU	KURU	KURU
27	KURU	KURU	KURU	KURU	0.870	0.503	0.408	KURU	KURU	KURU	KURU	KURU
28	KURU	KURU	KURU	KURU	0.710	0.503	0.325	KURU	KURU	KURU	KURU	KURU
29	KURU	KURU	KURU	KURU	-----	0.408	0.121	KURU	KURU	KURU	KURU	KURU
30	KURU	KURU	KURU	KURU	-----	0.408	0.121	KURU	KURU	KURU	KURU	KURU
31	KURU	-----	KURU	KURU	-----	0.325	-----	KURU	-----	KURU	KURU	-----
Maks.	KURU	KURU	KURU	KURU	0.870	5.20	1.65	0.121	KURU	KURU	KURU	KURU
Min.	KURU	KURU	KURU	KURU	KURU	0.325	0.078	KURU	KURU	KURU	KURU	KURU
Ortalama	KURU	KURU	KURU	KURU	0.470	0.853	0.254	0.049	KURU	KURU	KURU	KURU
LT/SN/Km2	0.000	0.000	0.000	0.000	3.78	6.86	2.04	0.393	0.000	0.000	0.000	0.000
AKIM mm.	0.000	0.000	0.000	0.000	9.15	18.4	5.29	1.05	0.000	0.000	0.000	0.000
MİL. M3	0.000	0.000	0.000	0.000	1.14	2.29	0.658	0.131	0.000	0.000	0.000	0.000

SU YILI (2006) YILLIK TOPLAM AKIM 4.22 MİLYON M3 34 MM. 1.1 LT/SN/Km2

16. Konya Kapali Havzasi

D16A126 Konya Ana Tah.Kan. Gölyazi

YERİ : **CİHANBEYLI GÖLYAZI BELDESI.**
33°12'2" Doğu - 38°33'23" Kuzey

YAĞIŞ ALANI : **1000,00 km2** **YAKLAŞIK KOT : 910 m**

GÖZLEM SÜRESİ : **01.02.1979 - 30.09.2006**

ORTALAMA AKIMLAR : **Gözlem süresinde 2.348 m3/sn. (25 Yıllık) 2006 Su yılında 0.376 m3/sn.**

ANLIK EN ÇOK VE EN AZ AKIMLAR:

2006 Su yılında anlık ençok akım	**:**	**3.08**	**m3/sn**	**13.02.2006**
2006 Su yılında anlık enaz akım	**:**	**0.021**	**m3/sn**	**31.08.2006**
Gözlem süresinde anlık ençok akım	**:**	**58.0**	**m3/sn**	**21.04.1988**
Gözlem süresinde anlık enaz akım	**:**	**0.000**	**m3/sn**	**01.09.1979**

İstasyon için kullanılmış anahtar bulunamadı.

Akımlar 01 Ekim 2005 'den 30 Eylül 2006' a kadar m3/sn olarak

Gün	Ekim	Kasım	Aralık	Ocak	Şubat	Mart	Nisan	Mayıs	Haziran	Temmuz	Ağustos	Eylül
01	0.132	0.132	0.285	0.454	0.285	1.14	0.722	0.722	0.183	0.098	0.038	0.038
02	0.132	0.132	0.285	0.543	0.285	1.02	0.543	0.900	0.183	0.098	0.038	0.038
03	0.132	0.132	0.285	0.543	0.285	1.02	0.722	1.02	0.183	0.066	0.038	0.038
04	0.132	0.234	0.285	0.543	0.370	0.900	0.632	0.900	0.183	0.066	0.038	0.038
05	0.132	0.234	0.285	0.454	0.285	0.900	0.632	0.900	0.132	0.066	0.038	0.038
06	0.132	0.234	0.285	0.454	0.370	0.900	0.632	0.900	0.132	0.066	0.021	0.038
07	0.132	0.234	0.285	0.543	0.370	0.811	0.632	0.811	0.132	0.066	0.021	0.038
08	0.132	0.234	0.285	0.454	0.370	0.722	0.454	0.811	0.132	0.066	0.021	0.038
09	0.098	0.183	0.285	0.454	0.285	0.722	0.454	0.722	0.132	0.066	0.021	0.038
10	0.098	0.183	0.370	0.454	0.370	0.722	0.632	0.722	0.132	0.066	0.021	0.038
11	0.098	0.234	0.370	0.454	0.722	0.632	0.543	0.632	0.132	0.066	0.021	0.038
12	0.098	0.234	0.370	0.370	1.26	0.632	0.543	0.543	0.132	0.066	0.038	0.038
13	0.132	0.234	0.454	0.370	2.56	0.543	0.543	0.543	0.132	0.066	0.038	0.038
14	0.132	0.234	0.454	0.454	2.30	0.632	0.632	0.543	0.132	0.066	0.038	0.038
15	0.098	0.234	0.454	0.370	2.14	0.632	0.632	0.454	0.132	0.066	0.038	0.038
16	0.098	0.234	0.454	0.370	1.98	0.632	0.543	0.454	0.132	0.066	0.038	0.038
17	0.098	0.234	0.543	0.370	1.98	0.722	0.543	0.454	0.132	0.066	0.038	0.038
18	0.132	0.234	0.543	0.370	1.82	0.811	0.543	0.370	0.132	0.066	0.038	0.038
19	0.132	0.234	0.543	0.285	1.82	1.02	0.543	0.370	0.132	0.038	0.038	0.038
20	0.132	0.234	0.543	0.285	1.66	1.02	0.543	0.370	0.098	0.066	0.038	0.038
21	0.132	0.285	0.543	0.370	1.82	1.14	0.454	0.370	0.098	0.066	0.038	0.038
22	0.132	0.285	0.543	0.370	1.66	1.14	0.454	0.285	0.098	0.066	0.038	0.066
23	0.132	0.285	0.543	0.285	1.50	1.02	0.370	0.285	0.098	0.066	0.021	0.038
24	0.132	0.285	0.543	0.370	1.50	1.02	0.722	0.234	0.098	0.038	0.021	0.066
25	0.132	0.285	0.543	0.285	1.26	0.900	0.722	0.234	0.098	0.038	0.038	0.066
26	0.132	0.285	0.543	0.370	1.14	0.900	0.811	0.234	0.098	0.038	0.038	0.066
27	0.132	0.285	0.454	0.285	1.26	0.811	0.811	0.234	0.098	0.038	0.038	0.066
28	0.132	0.285	0.370	0.285	1.14	0.811	0.722	0.234	0.098	0.038	0.038	0.066
29	0.132	0.285	0.370	0.370	-----	0.811	0.722	0.234	0.098	0.038	0.038	0.066
30	0.132	0.285	0.370	0.285	-----	0.811	0.722	0.234	0.098	0.038	0.038	0.066
31	0.132	-----	0.454	0.285	-----	0.722	-----	0.234	-----	0.038	0.038	-----
Maks.	0.183	0.370	0.543	0.543	3.08	1.50	1.50	1.02	0.285	0.098	0.098	0.132
Min.	0.066	0.098	0.285	0.285	0.285	0.543	0.234	0.183	0.098	0.038	0.021	0.038
Ortalama	0.124	0.237	0.417	0.392	1.17	0.846	0.606	0.515	0.126	0.060	0.034	0.045
LT/SN/Km2	0.124	0.237	0.417	0.392	1.17	0.846	0.606	0.515	0.126	0.060	0.034	0.045
AKIM mm.	0.333	0.615	1.12	1.05	2.83	2.27	1.57	1.38	0.327	0.161	0.090	0.118
MİL. M3	0.333	0.615	1.12	1.05	2.83	2.27	1.57	1.38	0.327	0.161	0.090	0.118

SU YILI (2006) YILLIK TOPLAM AKIM 11.86 MİLYON M3 12 MM. 0.4 LT/SN/Km2

16. Konya Kapali Havzasi

D16A134 Kocadere Derebucak

YERİ : **KONYA DEREBUCAK.**
31°31'9" Doğu - 37°23'1" Kuzey

YAĞIŞ ALANI : **173,00 km2** **YAKLAŞIK KOT : 1250 m**

GÖZLEM SÜRESİ : **01.10.1982 - 30.09.2006**

ORTALAMA AKIMLAR : **Gözlem süresinde 3.322 m3/sn. (15 Yıllık) 2006 Su yılında 3.290 m3/sn.**

ANLIK EN ÇOK VE EN AZ AKIMLAR:

2006 Su yılında anlık ençok akım	**:**	**39.3**	**m3/sn**	**11.02.2006**
2006 Su yılında anlık enaz akım	**:**	**0.000**	**m3/sn**	**01.10.2005**
Gözlem süresinde anlık ençok akım	**:**	**195.**	**m3/sn**	**26.12.2001**
Gözlem süresinde anlık enaz akım	**:**	**0.000**	**m3/sn**	**01.10.1985**

İstasyon için kullanılmış anahtar bulunamadı.

Akımlar 01 Ekim 2005 'den 30 Eylül 2006' a kadar m3/sn olarak

Gün	Ekim	Kasım	Aralık	Ocak	Şubat	Mart	Nisan	Mayıs	Haziran	Temmuz	Ağustos	Eylül
01	KURU	KURU	0.027	0.140	0.460	20.8	16.8	2.98	0.978	0.294	0.026	KURU
02	KURU	KURU	0.017	0.140	0.418	20.8	15.0	2.87	0.830	0.294	0.009	KURU
03	KURU	KURU	0.010	0.112	0.376	26.2	13.3	2.76	0.830	0.294	0.011	KURU
04	KURU	KURU	0.008	0.099	0.250	24.1	11.9	2.98	0.756	0.294	0.002	KURU
05	KURU	KURU	0.005	0.085	0.376	19.3	9.56	2.76	0.756	0.323	KURU	KURU
06	KURU	KURU	0.001	0.112	1.13	17.9	9.85	2.65	0.682	0.323	KURU	KURU
07	KURU	KURU	KURU	0.418	3.52	18.8	9.85	2.65	0.682	0.294	KURU	KURU
08	KURU	KURU	KURU	0.460	5.12	20.2	10.4	2.65	0.608	0.235	KURU	KURU
09	KURU	KURU	KURU	0.534	3.68	17.0	9.28	2.43	0.534	0.206	KURU	KURU
10	KURU	KURU	KURU	0.460	3.09	11.9	7.78	2.32	0.534	0.206	KURU	KURU
11	KURU	KURU	KURU	0.376	20.5	9.85	7.55	2.32	0.534	0.206	KURU	KURU
12	KURU	KURU	KURU	0.292	33.1	10.4	8.01	2.21	0.418	0.186	KURU	KURU
13	KURU	KURU	KURU	0.250	20.5	18.8	8.01	2.21	0.376	0.186	KURU	KURU
14	KURU	KURU	KURU	0.228	10.7	26.6	8.01	2.10	0.738	0.186	KURU	KURU
15	KURU	KURU	KURU	0.162	6.40	18.5	8.01	2.01	0.738	0.147	KURU	KURU
16	KURU	KURU	KURU	0.140	4.48	16.2	12.7	1.92	0.738	0.107	KURU	KURU
17	KURU	0.140	KURU	0.112	3.68	15.3	9.28	1.74	0.672	0.127	KURU	KURU
18	KURU	2.98	0.206	0.099	3.09	15.3	6.63	1.74	0.606	0.127	KURU	KURU
19	KURU	8.70	16.5	0.099	3.20	15.3	6.08	1.65	0.540	0.094	KURU	KURU
20	KURU	7.55	11.0	0.682	3.84	13.6	6.08	1.65	0.502	0.107	KURU	KURU
21	KURU	2.01	4.48	0.756	5.60	13.3	5.76	1.65	0.502	0.107	KURU	KURU
22	KURU	1.47	2.43	0.460	7.78	14.5	5.12	1.47	0.502	0.094	KURU	KURU
23	KURU	0.978	1.65	0.682	9.85	17.6	4.80	1.47	0.502	0.069	KURU	KURU
24	KURU	0.418	1.13	0.978	12.7	21.6	4.64	1.47	0.465	0.069	KURU	KURU
25	KURU	0.228	0.608	0.608	17.0	27.8	4.32	1.47	0.427	0.057	KURU	KURU
26	KURU	0.140	0.376	0.682	21.9	19.6	3.68	1.38	0.390	0.069	KURU	KURU
27	KURU	0.099	0.250	0.682	28.6	17.0	2.98	1.29	0.427	0.069	KURU	KURU
28	KURU	0.063	0.206	0.608	21.9	16.2	2.98	1.29	0.390	0.069	KURU	KURU
29	KURU	0.040	0.206	0.534	-----	15.9	2.98	1.20	0.390	0.057	KURU	KURU
30	KURU	0.027	0.206	0.534	-----	14.7	2.98	1.13	0.352	0.069	KURU	KURU
31	KURU	-----	0.184	0.534	-----	17.9	-----	0.978	-----	0.035	KURU	-----
Maks.	KURU	14.7	19.6	1.47	39.3	35.6	23.3	10.1	1.05	0.352	0.035	KURU
Min.	KURU	KURU	KURU	0.085	0.228	9.28	1.65	0.140	0.352	0.035	KURU	KURU
Ortalama	KURU	0.828	1.27	0.389	9.04	17.8	7.81	1.98	0.580	0.161	0.002	KURU
LT/SN/Km2	0.000	4.79	7.37	2.25	52.3	103.	45.1	11.4	3.35	0.932	0.009	0.000
AKIM mm.	0.000	12.4	19.7	6.02	126.	276.	117.	30.7	8.69	2.50	0.024	0.000
MİL. M3	0.000	2.15	3.41	1.04	21.9	47.8	20.2	5.30	1.50	0.432	0.004	0.000

SU YILI (2006) YILLIK TOPLAM AKIM 103.74 MİLYON M3 600 MM. 19.0 LT/SN/Km2

16. Konya Kapali Havzasi

D16A135 Tekke D. Mahmuthisar

YERİ : **ILGIN MAHMUTHİSAR KÖYÜ.**
32°1'41" Doğu - 38°11'26" Kuzey

YAĞIŞ ALANI : **66,40 km2** **YAKLAŞIK KOT : 1090 m**

GÖZLEM SÜRESİ : **01.01.1984 - 30.09.2006**

ORTALAMA AKIMLAR : **Gözlem süresinde 0.644 m3/sn. (22 Yıllık) 2006 Su yılında 0.542 m3/sn.**

ANLIK EN ÇOK VE EN AZ AKIMLAR:

2006 Su yılında anlık ençok akım	**:**	**26.1**	**m3/sn**	**24.04.2006**
2006 Su yılında anlık enaz akım	**:**	**0.140**	**m3/sn**	**20.04.2006**
Gözlem süresinde anlık ençok akım	**:**	**48.3**	**m3/sn**	**14.07.1995**
Gözlem süresinde anlık enaz akım	**:**	**0.000**	**m3/sn**	**01.10.1985**

İstasyon için kullanılmış anahtar bulunamadı.

Akımlar 01 Ekim 2005 'den 30 Eylül 2006' a kadar m3/sn olarak

Gün	Ekim	Kasım	Aralık	Ocak	Şubat	Mart	Nisan	Mayıs	Haziran	Temmuz	Ağustos	Eylül
01	0.320	0.414	0.410	0.480	0.410	0.950	0.840	0.740	0.320	1.03	0.320	0.200
02	0.320	0.414	0.410	0.410	0.410	0.840	0.740	0.740	0.320	1.03	0.320	0.260
03	0.320	0.414	0.340	0.410	0.340	0.840	0.740	0.740	0.320	0.911	0.320	0.260
04	0.320	0.414	0.340	0.480	0.340	0.840	0.740	0.740	0.260	0.695	0.320	0.200
05	0.320	0.414	0.410	0.480	0.340	0.740	0.660	1.83	0.320	0.508	0.320	0.140
06	0.320	0.508	0.410	0.480	0.340	0.740	0.580	1.28	0.320	0.508	0.320	0.140
07	0.320	0.601	0.410	0.480	0.480	0.740	0.580	1.28	0.260	0.508	0.320	0.200
08	0.320	0.601	0.410	0.480	0.480	0.840	0.480	1.28	0.320	0.414	0.320	0.200
09	0.414	0.601	0.410	0.480	0.410	0.840	0.580	1.28	0.414	0.140	0.260	0.200
10	0.414	0.601	0.410	0.480	0.410	0.840	0.580	1.16	0.414	0.140	0.260	0.200
11	0.414	0.601	0.410	0.480	0.580	0.740	0.480	1.16	0.508	0.140	0.260	0.200
12	0.320	0.601	0.410	0.480	0.660	0.740	0.410	1.16	0.508	0.140	0.200	0.200
13	0.414	0.601	0.410	0.480	0.740	0.840	0.340	1.16	0.508	0.140	0.200	0.200
14	0.508	0.601	0.410	0.480	0.740	0.840	0.230	1.16	0.601	0.140	0.200	0.200
15	0.508	0.508	0.410	0.480	0.740	0.840	0.410	1.16	0.601	0.200	0.140	0.200
16	0.601	0.508	0.410	0.410	0.660	0.840	0.580	1.16	0.695	0.260	0.140	0.200
17	0.789	0.414	0.410	0.410	0.580	0.740	0.580	1.16	0.695	0.260	0.140	0.140
18	0.789	0.508	0.480	0.410	0.740	0.740	0.580	1.16	0.601	0.260	0.140	0.200
19	0.789	0.508	0.480	0.410	0.840	0.840	0.580	1.03	0.508	0.260	0.200	0.200
20	0.789	0.508	0.480	0.410	0.840	1.05	0.480	0.911	0.508	0.260	0.200	0.140
21	0.695	0.410	0.480	0.410	0.950	1.05	0.410	0.911	0.508	0.260	0.200	0.200
22	0.601	0.290	0.480	0.410	0.950	0.840	0.480	0.911	0.320	0.260	0.200	0.200
23	0.508	0.230	0.580	0.410	0.950	0.740	0.950	0.789	0.260	0.320	0.200	0.260
24	0.508	0.230	0.480	0.410	0.840	0.740	9.50	0.789	0.260	0.320	0.200	0.320
25	0.508	0.230	0.480	0.410	0.740	0.740	2.30	0.601	0.260	0.260	0.200	0.320
26	0.508	0.290	0.480	0.410	0.740	0.950	1.20	0.911	0.260	0.200	0.200	0.320
27	0.320	0.230	0.480	0.410	0.950	0.840	1.05	2.11	0.260	0.200	0.140	0.320
28	0.320	0.290	0.480	0.410	0.950	0.840	0.950	1.16	0.320	0.260	0.140	0.414
29	0.320	0.290	0.480	0.410	-----	0.740	0.840	0.601	1.28	0.260	0.140	0.320
30	0.414	0.340	0.480	0.410	-----	0.660	0.740	0.320	1.03	0.260	0.140	0.320
31	0.414	-----	0.480	0.410	-----	0.740	-----	0.320	-----	0.260	0.140	-----
Maks.	1.03	3.33	0.950	0.480	1.65	1.35	26.1	3.87	10.3	1.40	0.320	0.414
Min.	0.260	0.230	0.340	0.340	0.340	0.410	0.140	0.320	0.200	0.140	0.140	0.140
Ortalama	0.465	0.439	0.440	0.439	0.648	0.816	0.987	1.02	0.459	0.349	0.219	0.229
LT/SN/Km2	7.01	6.61	6.63	6.62	9.76	12.3	14.9	15.4	6.91	5.25	3.30	3.45
AKIM mm.	18.8	17.1	17.8	17.7	23.6	32.9	38.5	41.3	17.9	14.1	8.85	8.94
MİL. M3	1.25	1.14	1.18	1.18	1.57	2.19	2.56	2.74	1.19	0.933	0.588	0.594

SU YILI (2006) YILLIK TOPLAM AKIM 17.12 MİLYON M3 258 MM. 8.2 LT/SN/Km2

16. Konya Kapali Havzasi

D16A136 Eldes D. Eldes

YERİ : **ILGIN ELDEŞ KÖYÜ.**
31°59'19" Doğu - 38°11'53" Kuzey

YAĞIŞ ALANI : **32,40 km2** **YAKLAŞIK KOT : 1080 m**

GÖZLEM SÜRESİ : **01.01.1984 - 30.09.2006**

ORTALAMA AKIMLAR : **Gözlem süresinde 0.242 m3/sn. (20 Yıllık) 2006 Su yılında 0.200 m3/sn.**

ANLIK EN ÇOK VE EN AZ AKIMLAR:

2006 Su yılında anlık ençok akım	**:**	**4.28**	**m3/sn**	**24.04.2006**
2006 Su yılında anlık enaz akım	**:**	**0.003**	**m3/sn**	**04.10.2005**
Gözlem süresinde anlık ençok akım	**:**	**7.61**	**m3/sn**	**03.08.2001**
Gözlem süresinde anlık enaz akım	**:**	**0.000**	**m3/sn**	**10.08.2004**

İstasyon için kullanılmış anahtar bulunamadı.

Akımlar 01 Ekim 2005 'den 30 Eylül 2006' a kadar m3/sn olarak

Gün	Ekim	Kasım	Aralık	Ocak	Şubat	Mart	Nisan	Mayıs	Haziran	Temmuz	Ağustos	Eylül
01	0.010	0.050	0.247	0.198	0.150	0.350	0.343	0.541	0.150	0.300	0.058	0.040
02	0.010	0.030	0.247	0.198	0.150	0.350	0.343	0.642	0.150	0.210	0.040	0.040
03	0.006	0.017	0.247	0.198	0.150	0.300	0.343	0.642	0.125	0.250	0.040	0.040
04	0.003	0.030	0.295	0.150	0.150	0.350	0.343	0.642	0.100	0.250	0.040	0.058
05	0.010	0.050	0.295	0.198	0.150	0.350	0.343	0.541	0.125	0.250	0.040	0.040
06	0.010	0.072	0.247	0.198	0.150	0.390	0.295	0.642	0.125	0.210	0.040	0.040
07	0.010	0.072	0.247	0.150	0.150	0.390	0.343	0.642	0.150	0.170	0.040	0.040
08	0.006	0.072	0.247	0.198	0.150	0.350	0.343	0.541	0.125	0.105	0.040	0.040
09	0.006	0.072	0.247	0.150	0.150	0.390	0.295	0.642	0.150	0.105	0.040	0.040
10	0.006	0.072	0.247	0.150	0.125	0.450	0.295	0.541	0.198	0.080	0.058	0.040
11	0.010	0.072	0.247	0.150	0.198	0.390	0.343	0.541	0.390	0.080	0.058	0.058
12	0.010	0.072	0.247	0.150	0.198	0.450	0.295	0.541	0.390	0.058	0.040	0.058
13	0.010	0.072	0.247	0.150	0.198	0.450	0.295	0.541	0.300	0.080	0.040	0.058
14	0.010	0.125	0.247	0.150	0.150	0.450	0.295	0.440	0.210	0.040	0.040	0.058
15	0.010	0.150	0.247	0.150	0.150	0.450	0.343	0.440	0.210	0.058	0.040	0.058
16	0.010	0.150	0.247	0.150	0.150	0.450	0.295	0.541	0.170	0.040	0.058	0.058
17	0.010	0.150	0.247	0.150	0.150	0.450	0.247	0.440	0.170	0.040	0.058	0.058
18	0.010	0.295	0.247	0.150	0.198	0.520	0.247	0.440	0.210	0.040	0.058	0.058
19	0.010	0.247	0.247	0.150	0.198	0.520	0.247	0.440	0.140	0.040	0.058	0.058
20	0.010	0.247	0.247	0.150	0.198	0.440	0.247	0.392	0.140	0.040	0.058	0.058
21	0.017	0.343	0.247	0.150	0.198	0.392	0.247	0.440	0.170	0.040	0.058	0.080
22	0.017	0.295	0.247	0.150	0.150	0.392	0.247	0.392	0.140	0.027	0.058	0.080
23	0.030	0.198	0.198	0.150	0.350	0.343	0.247	0.392	0.140	0.040	0.058	0.058
24	0.030	0.198	0.198	0.150	0.350	0.392	2.14	0.343	0.080	0.040	0.040	0.105
25	0.017	0.198	0.247	0.150	0.350	0.343	0.642	0.392	0.058	0.040	0.040	0.140
26	0.017	0.247	0.247	0.150	0.300	0.343	0.541	0.343	0.058	0.058	0.027	0.105
27	0.072	0.247	0.198	0.150	0.300	0.343	0.541	0.247	0.058	0.058	0.027	0.105
28	0.017	0.247	0.198	0.150	0.350	0.343	0.440	0.198	0.058	0.058	0.027	0.140
29	0.030	0.247	0.247	0.125	-----	0.295	0.541	0.150	0.210	0.058	0.027	0.140
30	0.050	0.247	0.247	0.150	-----	0.295	0.541	0.150	0.300	0.058	0.027	0.140
31	0.050	-----	0.198	0.150	-----	0.295	-----	0.150	-----	0.058	0.027	-----
Maks.	0.072	0.440	0.343	0.295	0.350	0.520	4.28	0.945	1.85	0.390	0.140	0.250
Min.	0.003	0.017	0.198	0.100	0.125	0.295	0.198	0.125	0.058	0.016	0.016	0.040
Ortalama	0.017	0.153	0.242	0.158	0.200	0.388	0.409	0.451	0.167	0.096	0.044	0.070
LT/SN/Km2	0.522	4.72	7.48	4.89	6.18	12.0	12.6	13.9	5.14	2.97	1.35	2.15
AKIM mm.	1.40	12.2	20.0	13.1	15.0	32.0	32.7	37.3	13.3	7.95	3.63	5.58
MİL. M3	0.045	0.396	0.649	0.424	0.485	1.04	1.06	1.21	0.432	0.258	0.118	0.181

SU YILI (2006) YILLIK TOPLAM AKIM 6.30 MİLYON M3 194 MM. 6.2 LT/SN/Km2

16. Konya Kapali Havzasi

D16A137 Bulcuk D. Bulcuk

YERİ : **ILGIN BULCUK KARAYOLU ÜZERİ.**
31°56'35" Doğu - 38°12'44" Kuzey

YAĞIŞ ALANI : **87,70 km2** **YAKLAŞIK KOT : 1080 m**

GÖZLEM SÜRESİ : **01.01.1984 - 30.09.2006**

ORTALAMA AKIMLAR : **Gözlem süresinde 0.327 m3/sn. (21 Yıllık) 2006 Su yılında 0.214 m3/sn.**

ANLIK EN ÇOK VE EN AZ AKIMLAR:

2006 Su yılında anlık ençok akım	**:**	**19.9**	**m3/sn**	**24.04.2006**
2006 Su yılında anlık enaz akım	**:**	**0.000**	**m3/sn**	**27.10.2005**
Gözlem süresinde anlık ençok akım	**:**	**19.9**	**m3/sn**	**24.04.2006**
Gözlem süresinde anlık enaz akım	**:**	**0.000**	**m3/sn**	**07.07.1985**

İstasyon için kullanılmış anahtar bulunamadı.

Akımlar 01 Ekim 2005 'den 30 Eylül 2006' a kadar m3/sn olarak

Gün	Ekim	Kasım	Aralık	Ocak	Şubat	Mart	Nisan	Mayıs	Haziran	Temmuz	Ağustos	Eylül
01	0.032	KURU	0.087	0.053	0.016	0.660	0.433	0.660	0.087	0.078	0.125	0.048
02	0.032	KURU	0.087	0.053	0.016	0.660	0.433	0.660	0.087	0.078	0.125	0.048
03	0.032	KURU	0.087	0.053	0.032	0.660	0.433	0.660	0.087	0.125	0.125	0.048
04	0.032	KURU	0.087	0.053	0.032	0.660	0.433	0.660	0.087	0.078	0.125	0.048
05	0.016	0.006	0.087	0.053	0.032	0.546	0.433	0.660	0.087	0.125	0.125	0.048
06	0.048	0.006	0.087	0.053	0.006	0.433	0.433	0.546	0.087	0.125	0.125	0.048
07	0.025	0.006	0.087	0.053	0.006	0.433	0.356	0.546	0.087	0.125	0.125	0.048
08	0.025	0.006	0.087	0.053	0.006	0.433	0.356	0.546	0.087	0.078	0.125	0.048
09	0.025	0.006	0.087	0.087	0.006	0.433	0.356	0.520	0.087	0.078	0.125	0.048
10	0.011	0.001	0.087	0.087	0.087	0.433	0.356	0.425	0.087	0.078	0.125	0.048
11	0.011	0.001	0.087	0.087	0.660	0.356	0.356	0.329	0.087	0.078	0.078	0.048
12	0.011	0.001	0.053	0.087	0.887	0.356	0.273	0.259	0.087	0.078	0.078	0.053
13	0.011	0.006	0.053	0.087	0.887	0.356	0.273	0.259	0.087	0.078	0.078	0.053
14	0.011	0.006	0.053	0.087	0.773	0.433	0.273	0.259	0.087	0.125	0.078	0.053
15	0.011	0.006	0.053	0.087	0.773	0.546	0.273	0.259	0.087	0.125	0.125	0.032
16	0.011	0.006	0.053	0.087	0.773	0.546	0.273	0.259	0.087	0.125	0.125	0.032
17	0.011	0.006	0.053	0.087	0.660	0.546	0.356	0.329	0.087	0.125	0.125	0.032
18	0.011	0.006	0.053	0.087	0.660	0.546	0.273	0.190	0.087	0.125	0.125	0.032
19	0.011	0.006	0.053	0.087	0.773	0.660	0.273	0.190	0.087	0.125	0.125	0.032
20	0.011	0.006	0.053	0.087	0.887	0.546	0.273	0.190	0.053	0.125	0.078	0.016
21	0.011	0.016	0.190	0.087	1.16	0.660	0.273	0.190	0.087	0.078	0.078	0.032
22	0.011	0.016	0.087	0.087	1.00	0.546	0.273	0.190	0.087	0.125	0.078	0.032
23	0.011	0.032	0.087	0.087	0.887	0.433	0.433	0.190	0.053	0.125	0.078	0.032
24	0.011	0.032	0.120	0.087	0.660	0.660	8.90	0.190	0.053	0.125	0.048	0.032
25	0.011	0.032	0.120	0.087	0.773	0.660	1.62	0.120	0.053	0.125	0.048	0.032
26	0.011	0.032	0.032	0.087	0.660	0.660	0.887	0.120	0.053	0.125	0.048	0.032
27	0.003	0.032	0.006	0.087	0.773	0.546	0.773	0.190	0.053	0.125	0.048	0.016
28	KURU	0.032	0.016	0.032	0.660	0.433	0.660	0.190	0.053	0.125	0.048	0.016
29	KURU	0.053	0.053	0.016	-----	0.433	0.660	0.120	0.053	0.125	0.048	0.016
30	KURU	0.087	0.053	0.016	-----	0.433	0.660	0.120	0.125	0.125	0.048	0.016
31	KURU	-----	0.053	0.016	-----	0.433	-----	0.120	-----	0.125	0.048	-----
Maks.	0.048	0.087	0.616	0.190	1.62	1.00	19.9	0.773	0.125	0.186	0.125	0.078
Min.	KURU	KURU	0.006	0.016	0.006	0.273	0.273	0.032	0.053	0.078	0.025	0.006
Ortalama	0.015	0.015	0.073	0.070	0.519	0.521	0.735	0.327	0.079	0.110	0.093	0.037
LT/SN/Km2	0.168	0.169	0.828	0.793	5.92	5.94	8.38	3.73	0.903	1.25	1.06	0.425
AKIM mm.	0.450	0.438	2.22	2.13	14.3	15.9	21.7	10.00	2.34	3.35	2.84	1.10
MİL. M3	0.039	0.038	0.194	0.186	1.26	1.39	1.91	0.877	0.205	0.294	0.249	0.097

SU YILI (2006) YILLIK TOPLAM AKIM 6.74 MİLYON M3 77 MM. 2.4 LT/SN/Km2

16. Konya Kapali Havzasi

D16A138 Seki D. Derebucak

YERİ : **KONYA DEREBUCAK.**
31°29'50" Doğu - 37°25'22" Kuzey

YAĞIŞ ALANI : **38,00 km2** **YAKLAŞIK KOT : 1225 m**

GÖZLEM SÜRESİ : **01.10.1984 - 30.09.2006**

ORTALAMA AKIMLAR : **Gözlem süresinde 0.297 m3/sn. (22 Yıllık) 2006 Su yılında 0.211 m3/sn.**

ANLIK EN ÇOK VE EN AZ AKIMLAR:

2006 Su yılında anlık ençok akım	:	**5.40**	**m3/sn**	**11.02.2006**
2006 Su yılında anlık enaz akım	:	**0.000**	**m3/sn**	**01.10.2005**
Gözlem süresinde anlık ençok akım	:	**25.0**	**m3/sn**	**17.12.1987**
Gözlem süresinde anlık enaz akım	:	**0.000**	**m3/sn**	**01.10.1984**

İstasyon için kullanılmış anahtar bulunamadı.

Akımlar 01 Ekim 2005 'den 30 Eylül 2006' a kadar m3/sn olarak

Gün	Ekim	Kasım	Aralık	Ocak	Şubat	Mart	Nisan	Mayıs	Haziran	Temmuz	Ağustos	Eylül
01	KURU	KURU	KURU	0.068	0.068	1.45	0.560	0.068	KURU	KURU	KURU	KURU
02	KURU	KURU	KURU	0.068	0.068	1.30	0.500	0.068	KURU	KURU	KURU	0.018
03	KURU	KURU	KURU	0.068	0.068	1.35	0.420	0.090	KURU	0.031	KURU	KURU
04	KURU	KURU	KURU	0.068	0.068	1.30	0.370	0.068	KURU	0.068	KURU	KURU
05	KURU	KURU	KURU	0.068	0.068	1.15	0.340	0.068	KURU	0.031	KURU	KURU
06	KURU	KURU	KURU	0.068	0.140	0.860	0.300	0.068	KURU	0.018	KURU	KURU
07	KURU	KURU	KURU	0.068	0.640	0.820	0.260	0.068	KURU	0.018	KURU	KURU
08	KURU	KURU	KURU	0.140	0.760	0.980	0.230	0.049	KURU	0.018	KURU	KURU
09	KURU	KURU	KURU	0.140	0.420	1.25	0.200	0.049	KURU	0.018	KURU	KURU
10	KURU	KURU	KURU	0.090	0.420	0.940	0.200	0.031	KURU	0.018	KURU	KURU
11	KURU	KURU	KURU	0.090	3.00	0.820	0.155	0.031	KURU	0.018	KURU	KURU
12	KURU	KURU	KURU	0.090	2.90	0.760	0.140	KURU	KURU	0.018	KURU	KURU
13	KURU	KURU	KURU	0.090	1.25	1.50	0.115	KURU	KURU	0.018	KURU	KURU
14	KURU	KURU	KURU	0.090	0.760	4.10	0.115	KURU	KURU	0.018	KURU	KURU
15	KURU	KURU	KURU	0.090	0.560	2.90	0.115	KURU	KURU	0.018	KURU	KURU
16	KURU	KURU	KURU	0.090	0.500	2.40	0.140	KURU	KURU	0.018	KURU	KURU
17	KURU	KURU	KURU	0.090	0.420	2.10	0.115	KURU	KURU	0.031	KURU	KURU
18	KURU	KURU	KURU	0.090	0.420	1.85	0.090	KURU	KURU	KURU	KURU	KURU
19	KURU	KURU	0.370	0.090	0.560	1.70	0.090	KURU	KURU	KURU	KURU	KURU
20	KURU	KURU	0.340	0.090	0.560	1.45	0.090	KURU	KURU	KURU	KURU	KURU
21	KURU	0.049	0.200	0.090	0.560	1.10	0.090	KURU	KURU	KURU	KURU	KURU
22	KURU	0.090	0.140	0.090	0.560	0.980	0.090	KURU	KURU	KURU	KURU	KURU
23	KURU	0.090	0.140	0.090	0.560	0.980	0.090	KURU	KURU	KURU	KURU	KURU
24	KURU	0.200	0.115	0.140	1.25	1.05	0.090	KURU	KURU	KURU	KURU	KURU
25	KURU	0.115	0.115	0.115	1.65	1.80	0.090	KURU	KURU	KURU	KURU	KURU
26	KURU	0.068	0.115	0.115	1.60	1.25	0.068	KURU	KURU	KURU	KURU	KURU
27	KURU	0.068	0.090	0.115	1.85	0.940	0.068	KURU	KURU	KURU	KURU	KURU
28	KURU	0.068	0.090	0.115	1.60	0.820	0.049	KURU	KURU	KURU	KURU	KURU
29	KURU	0.049	0.090	0.090	-----	0.700	0.049	KURU	KURU	KURU	KURU	KURU
30	KURU	KURU	0.090	0.090	-----	0.640	0.049	KURU	KURU	KURU	KURU	KURU
31	KURU	-----	0.068	0.068	-----	0.640	-----	KURU	-----	KURU	KURU	-----
Maks.	KURU	0.200	0.600	0.155	5.40	4.90	0.640	0.090	KURU	0.090	0.031	0.049
Min.	KURU	KURU	KURU	0.068	0.068	0.640	0.049	KURU	KURU	KURU	KURU	KURU
Ortalama	KURU	0.027	0.063	0.092	0.831	1.35	0.176	0.021	KURU	0.012	KURU	0.001
LT/SN/Km2	0.000	0.699	1.67	2.43	21.9	35.6	4.63	0.559	0.000	0.305	0.000	0.016
AKIM mm.	0.000	1.81	4.46	6.51	52.9	95.2	12.0	1.50	0.000	0.816	0.000	0.041
MİL. M3	0.000	0.069	0.170	0.247	2.01	3.62	0.456	0.057	0.000	0.031	0.000	0.002

SU YILI (2006) YILLIK TOPLAM AKIM 6.66 MİLYON M3 175 MM. 5.6 LT/SN/Km2

16. Konya Kapali Havzasi

D16A139 Findikli D. Altinapa Brj.Giris

YERİ : 32°17'11" Doğu - 37°52'59" Kuzey

YAĞIŞ ALANI : 84,80 km2 **YAKLAŞIK KOT :** 1256 m

GÖZLEM SÜRESİ : 01.10.1984 - 30.09.2006

ORTALAMA AKIMLAR : Gözlem süresinde 0.046 m3/sn. (11 Yıllık) 2006 Su yılında 0.002 m3/sn.

ANLIK EN ÇOK VE EN AZ AKIMLAR:

2006 Su yılında anlık ençok akım	:	0.250 m3/sn	29.06.2006
2006 Su yılında anlık enaz akım	:	0.000 m3/sn	01.10.2005
Gözlem süresinde anlık ençok akım	:	4.10 m3/sn	06.07.1987
Gözlem süresinde anlık enaz akım	:	0.000 m3/sn	01.10.1984

İstasyon için kullanılmış anahtar bulunamadı.

Akımlar 01 Ekim 2005 'den 30 Eylül 2006' a kadar m3/sn olarak

Gün	Ekim	Kasım	Aralık	Ocak	Şubat	Mart	Nisan	Mayıs	Haziran	Temmuz	Ağustos	Eylül
01	KURU	KURU	KURU	KURU	KURU	KURU	KURU	0.009	KURU	0.009	KURU	KURU
02	KURU	KURU	KURU	KURU	KURU	KURU	KURU	0.007	KURU	KURU	KURU	KURU
03	KURU	KURU	KURU	KURU	KURU	KURU	KURU	0.006	KURU	KURU	KURU	KURU
04	KURU	KURU	KURU	KURU	KURU	KURU	KURU	0.004	KURU	KURU	KURU	KURU
05	KURU	KURU	KURU	KURU	KURU	KURU	KURU	0.004	KURU	KURU	KURU	KURU
06	KURU	KURU	KURU	KURU	KURU	KURU	KURU	0.004	KURU	KURU	KURU	KURU
07	KURU	KURU	KURU	KURU	KURU	KURU	KURU	0.002	KURU	KURU	KURU	KURU
08	KURU	KURU	KURU	KURU	KURU	KURU	KURU	0.002	KURU	KURU	KURU	KURU
09	KURU	KURU	KURU	KURU	KURU	KURU	KURU	0.002	KURU	KURU	KURU	KURU
10	KURU	KURU	KURU	KURU	KURU	KURU	KURU	0.002	KURU	KURU	KURU	KURU
11	KURU	KURU	KURU	KURU	KURU	KURU	KURU	0.002	KURU	KURU	KURU	KURU
12	KURU	KURU	KURU	KURU	KURU	KURU	KURU	0.002	KURU	KURU	KURU	KURU
13	KURU	KURU	KURU	KURU	KURU	KURU	KURU	0.002	KURU	KURU	KURU	KURU
14	0.004	KURU	KURU	KURU	KURU	KURU	KURU	0.002	KURU	KURU	KURU	KURU
15	0.022	KURU	KURU	KURU	KURU	KURU	KURU	0.002	KURU	KURU	KURU	KURU
16	0.009	KURU	KURU	KURU	KURU	KURU	KURU	0.002	KURU	KURU	KURU	KURU
17	0.004	KURU	KURU	KURU	KURU	KURU	KURU	0.004	KURU	KURU	KURU	KURU
18	KURU	KURU	KURU	KURU	KURU	KURU	KURU	0.006	KURU	KURU	KURU	KURU
19	KURU	KURU	KURU	KURU	KURU	KURU	KURU	0.006	KURU	KURU	KURU	KURU
20	KURU	KURU	KURU	KURU	KURU	KURU	KURU	0.006	KURU	KURU	KURU	KURU
21	KURU	KURU	KURU	KURU	KURU	KURU	KURU	0.006	KURU	KURU	KURU	KURU
22	KURU	KURU	KURU	KURU	KURU	KURU	KURU	0.006	KURU	KURU	KURU	KURU
23	KURU	KURU	KURU	KURU	KURU	KURU	0.018	0.006	KURU	KURU	KURU	KURU
24	KURU	KURU	KURU	KURU	KURU	KURU	0.145	0.006	KURU	KURU	KURU	KURU
25	KURU	KURU	KURU	KURU	KURU	KURU	0.067	0.004	KURU	KURU	KURU	KURU
26	KURU	KURU	KURU	KURU	KURU	KURU	0.043	0.004	KURU	KURU	KURU	KURU
27	KURU	KURU	KURU	KURU	KURU	KURU	0.035	0.002	KURU	KURU	KURU	KURU
28	KURU	KURU	KURU	KURU	KURU	KURU	0.027	0.002	KURU	KURU	KURU	KURU
29	KURU	KURU	KURU	KURU	-----	KURU	0.018	KURU	0.014	KURU	KURU	KURU
30	KURU	KURU	KURU	KURU	-----	KURU	0.012	KURU	0.012	KURU	KURU	KURU
31	KURU	-----	KURU	KURU	-----	KURU	-----	KURU	-----	KURU	KURU	-----
Maks.	0.035	KURU	KURU	KURU	KURU	KURU	0.198	0.018	0.250	0.009	KURU	KURU
Min.	KURU	KURU	KURU	KURU	KURU	KURU	KURU	KURU	KURU	KURU	KURU	KURU
Ortalama	0.001	KURU	KURU	KURU	KURU	KURU	0.012	0.004	0.001	0.000	KURU	KURU
LT/SN/Km2	0.015	0.000	0.000	0.000	0.000	0.000	0.143	0.043	0.010	0.003	0.000	0.000
AKIM mm.	0.040	0.000	0.000	0.000	0.000	0.000	0.372	0.114	0.026	0.009	0.000	0.000
MİL. M3	0.003	0.000	0.000	0.000	0.000	0.000	0.032	0.010	0.002	0.001	0.000	0.000

SU YILI (2006) YILLIK TOPLAM AKIM 0.05 MİLYON M3 1 MM. 0.0 LT/SN/Km2

16. Konya Kapali Havzasi

D16A140 Ivriz Ç. Aydinkent

YERİ : **EREĞLİ AYDINKENT KÖYÜ MEVKII.**
34°10'31" Doğu - 37°24'58" Kuzey

YAĞIŞ ALANI : **33,50 km2** **YAKLAŞIK KOT : 1161 m**

GÖZLEM SÜRESİ : **28.11.1984 - 30.09.2006**

ORTALAMA AKIMLAR : **Gözlem süresinde 3.848 m3/sn. (20 Yıllık) 2006 Su yılında 1.953 m3/sn.**

ANLIK EN ÇOK VE EN AZ AKIMLAR:

2006 Su yılında anlık ençok akım	**:**	**5.70**	**m3/sn**	**25.05.2006**
2006 Su yılında anlık enaz akım	**:**	**0.468**	**m3/sn**	**19.08.2006**
Gözlem süresinde anlık ençok akım	**:**	**16.5**	**m3/sn**	**18.06.1988**
Gözlem süresinde anlık enaz akım	**:**	**0.400**	**m3/sn**	**24.12.2002**

İstasyon için kullanılmış anahtar bulunamadı.

Akımlar 01 Ekim 2005 'den 30 Eylül 2006' a kadar m3/sn olarak

Gün	Ekim	Kasım	Aralık	Ocak	Şubat	Mart	Nisan	Mayıs	Haziran	Temmuz	Ağustos	Eylül
01	1.00	0.900	0.820	1.10	0.820	0.900	0.900	4.40	5.70	3.50	3.08	1.20
02	1.10	0.900	0.820	1.10	0.820	0.900	0.900	4.40	5.70	3.50	3.08	1.20
03	1.10	0.900	0.820	1.10	0.820	0.900	0.900	4.40	5.70	3.50	3.08	1.20
04	1.10	0.900	0.820	1.10	0.820	0.900	0.900	4.40	5.70	3.50	3.08	1.10
05	1.10	0.900	0.820	1.20	0.820	0.900	0.900	4.40	5.70	3.30	3.08	1.10
06	1.10	0.900	0.820	1.20	0.820	0.900	0.900	4.70	5.70	3.30	2.90	1.10
07	1.10	0.900	1.00	1.10	0.820	0.900	0.900	4.70	5.70	3.10	2.58	1.10
08	1.10	0.900	0.900	1.10	0.820	0.900	0.900	4.70	5.70	2.80	2.26	1.10
09	1.10	0.900	1.00	1.10	0.820	0.900	0.900	4.70	5.70	2.60	1.40	1.20
10	1.10	0.900	0.820	1.10	0.820	0.900	0.900	4.70	5.40	2.60	1.10	1.20
11	1.10	0.900	0.820	1.10	0.820	0.900	1.00	5.00	5.40	2.40	0.900	1.20
12	1.10	0.900	0.820	1.10	0.820	0.900	1.00	5.00	5.40	1.90	0.810	1.20
13	1.10	0.900	0.820	1.10	0.820	0.900	1.10	5.00	5.40	1.80	0.718	1.20
14	1.10	1.00	0.820	1.10	0.820	0.900	1.20	5.20	5.40	1.70	0.641	1.20
15	1.10	1.20	0.820	1.10	0.820	0.900	1.40	5.20	5.40	1.55	0.545	1.20
16	1.10	1.10	0.820	1.10	0.820	0.820	1.70	5.40	5.20	1.55	0.468	1.20
17	1.10	0.900	0.820	1.00	0.820	0.820	1.90	5.40	5.20	1.40	0.468	1.20
18	1.10	0.820	0.820	1.00	0.820	0.820	2.20	5.40	5.20	1.55	0.468	1.20
19	1.10	0.820	0.820	1.00	0.820	0.820	2.60	5.40	5.00	2.40	0.545	1.20
20	1.10	0.820	0.900	1.00	0.820	0.820	3.10	5.40	5.00	2.80	0.641	1.20
21	1.10	0.820	1.00	1.00	0.820	0.820	3.70	5.40	5.00	3.30	0.810	1.20
22	1.10	0.900	1.10	1.00	0.820	0.820	3.70	5.40	4.40	3.30	1.00	1.20
23	1.00	1.10	1.20	1.00	0.820	0.820	3.70	5.40	4.20	3.30	1.00	1.20
24	1.00	1.00	1.20	1.00	0.820	0.820	3.70	5.40	4.20	3.08	1.00	1.20
25	0.900	1.20	1.20	0.900	0.820	0.820	3.90	5.70	3.90	2.90	0.900	1.30
26	1.00	1.10	1.20	0.900	0.820	0.820	3.90	5.70	3.90	3.08	0.900	1.30
27	1.10	1.30	1.20	0.900	0.820	0.820	3.90	5.70	3.70	3.08	0.900	1.30
28	0.900	1.70	1.20	0.900	0.820	0.820	4.20	5.70	3.70	2.90	1.00	1.40
29	0.900	1.55	1.20	0.900	-----	0.820	4.20	5.70	3.70	2.90	1.55	1.30
30	0.900	1.20	1.20	0.900	-----	0.820	4.20	5.70	3.70	2.90	1.30	1.30
31	0.900	-----	1.20	0.900	-----	0.820	-----	5.70	-----	3.08	1.20	-----
Maks.	1.40	2.10	2.20	1.20	0.820	0.900	4.20	5.70	5.70	3.90	3.26	1.80
Min.	0.900	0.820	0.820	0.900	0.820	0.820	0.900	4.40	3.70	1.30	0.468	1.10
Ortalama	1.05	1.01	0.962	1.04	0.820	0.859	2.18	5.14	4.99	2.73	1.40	1.21
LT/SN/Km2	31.5	30.1	28.7	30.9	24.5	25.6	65.0	153.	149.	81.4	41.8	36.0
AKIM mm.	84.3	78.0	76.9	82.8	59.2	68.7	168.	411.	386.	218.	112.	93.4
MİL. M3	2.83	2.61	2.58	2.77	1.98	2.30	5.64	13.8	12.9	7.31	3.75	3.13

SU YILI (2006) YILLIK TOPLAM AKIM 61.60 MİLYON M3 1839 MM. 58.3 LT/SN/Km2

16. Konya Kapali Havzasi

D16A141 Zanapa D. Halkapinar

YERİ : **EREĞLİ HALKAPINAR(ZANAPA) BELDESI.**
34°11'37" Doğu - 37°25'48" Kuzey

YAĞIŞ ALANI : **273,00 km2** **YAKLAŞIK KOT : 1160 m**

GÖZLEM SÜRESİ : **01.10.1984 - 30.09.2006**

ORTALAMA AKIMLAR : **Gözlem süresinde 0.793 m3/sn. (19 Yıllık) 2006 Su yılında 0.109 m3/sn.**

ANLIK EN ÇOK VE EN AZ AKIMLAR:

2006 Su yılında anlık ençok akım	**:**	**17.6**	**m3/sn**	**22.04.2006**
2006 Su yılında anlık enaz akım	**:**	**0.000**	**m3/sn**	**01.10.2005**
Gözlem süresinde anlık ençok akım	**:**	**62.0**	**m3/sn**	**21.07.1991**
Gözlem süresinde anlık enaz akım	**:**	**0.000**	**m3/sn**	**01.10.1985**

İstasyon için kullanılmış anahtar bulunamadı.

Akımlar 01 Ekim 2005 'den 30 Eylül 2006' a kadar m3/sn olarak

Gün	Ekim	Kasım	Aralık	Ocak	Şubat	Mart	Nisan	Mayıs	Haziran	Temmuz	Ağustos	Eylül
01	KURU	KURU	0.100	KURU	KURU	KURU	KURU	0.219	0.173	0.383	KURU	KURU
02	KURU	KURU	0.100	KURU	KURU	KURU	0.334	0.195	0.152	0.173	KURU	KURU
03	KURU	KURU	0.100	KURU	KURU	KURU	0.880	0.970	0.131	0.173	KURU	KURU
04	KURU	KURU	0.100	KURU	KURU	KURU	0.700	1.76	0.100	0.215	KURU	KURU
05	KURU	KURU	0.100	KURU	KURU	KURU	0.654	0.887	0.100	0.194	KURU	KURU
06	KURU	KURU	0.100	KURU	KURU	KURU	0.517	0.572	0.079	0.110	KURU	KURU
07	KURU	0.288	0.100	KURU	KURU	KURU	0.172	0.320	0.068	0.058	KURU	KURU
08	KURU	0.471	0.100	KURU	KURU	KURU	0.242	0.446	0.058	KURU	KURU	KURU
09	KURU	0.425	0.113	KURU	KURU	KURU	0.425	0.383	0.052	KURU	KURU	KURU
10	KURU	0.334	0.125	KURU	KURU	KURU	1.15	0.257	0.046	KURU	KURU	KURU
11	KURU	0.288	0.125	KURU	KURU	KURU	1.24	0.572	0.046	KURU	KURU	KURU
12	KURU	0.242	0.125	KURU	KURU	KURU	1.33	0.278	0.039	KURU	KURU	KURU
13	KURU	0.148	0.125	KURU	KURU	KURU	0.700	0.236	0.052	KURU	KURU	KURU
14	KURU	0.088	0.125	KURU	KURU	KURU	0.219	0.278	KURU	KURU	KURU	KURU
15	KURU	0.100	0.125	KURU	KURU	KURU	0.242	0.446	KURU	KURU	KURU	KURU
16	KURU	0.075	0.113	KURU	KURU	KURU	0.880	0.236	KURU	KURU	KURU	KURU
17	KURU	0.043	0.113	KURU	KURU	KURU	0.700	0.215	KURU	KURU	KURU	KURU
18	KURU	0.037	0.100	KURU	KURU	KURU	0.288	0.194	KURU	KURU	KURU	KURU
19	KURU	0.037	0.100	KURU	KURU	KURU	0.075	0.194	KURU	KURU	KURU	KURU
20	KURU	0.037	0.088	KURU	KURU	KURU	0.100	0.194	KURU	KURU	KURU	KURU
21	KURU	0.050	0.088	KURU	KURU	KURU	0.125	0.194	KURU	KURU	KURU	KURU
22	KURU	0.075	0.075	KURU	KURU	KURU	0.880	0.194	KURU	KURU	KURU	KURU
23	KURU	0.100	0.063	KURU	KURU	KURU	2.86	0.299	KURU	KURU	KURU	KURU
24	KURU	0.100	0.063	KURU	KURU	KURU	0.970	0.215	KURU	KURU	KURU	KURU
25	KURU	0.100	0.063	KURU	KURU	KURU	1.51	0.236	KURU	KURU	KURU	KURU
26	KURU	0.100	0.075	KURU	0.063	KURU	0.471	0.194	KURU	KURU	KURU	KURU
27	KURU	0.100	0.043	KURU	0.063	KURU	0.288	0.194	KURU	KURU	KURU	KURU
28	KURU	0.100	KURU	KURU	0.063	KURU	0.195	0.194	KURU	KURU	KURU	KURU
29	KURU	0.100	KURU	KURU	-----	KURU	0.288	0.194	0.131	KURU	KURU	KURU
30	KURU	0.100	KURU	KURU	-----	KURU	0.425	0.194	0.950	KURU	KURU	KURU
31	KURU	-----	KURU	KURU	-----	KURU	-----	0.173	-----	KURU	KURU	-----
Maks.	KURU	0.517	0.125	KURU	0.100	KURU	17.6	3.91	15.0	2.90	KURU	KURU
Min.	KURU	KURU	KURU	KURU	KURU	KURU	KURU	0.173	KURU	KURU	KURU	KURU
Ortalama	KURU	0.118	0.085	KURU	0.007	KURU	0.629	0.359	0.073	0.042	KURU	KURU
LT/SN/Km2	0.000	0.432	0.313	0.000	0.025	0.000	2.30	1.32	0.266	0.154	0.000	0.000
AKIM mm.	0.000	1.12	0.838	0.000	0.060	0.000	5.97	3.52	0.689	0.413	0.000	0.000
MİL. M3	0.000	0.306	0.229	0.000	0.016	0.000	1.63	0.962	0.188	0.113	0.000	0.000

SU YILI (2006) YILLIK TOPLAM AKIM 3.44 MİLYON M3 13 MM. 0.4 LT/SN/Km2

16. Konya Kapali Havzasi

D16A148 Ören D. Gümüsler

YERİ : **NİĞDE GÜMÜŞLER BELDESI.**
34°47'47" Doğu - 37°58'16" Kuzey

YAĞIŞ ALANI : **44,60 km2** **YAKLAŞIK KOT : 1500 m**

GÖZLEM SÜRESİ : **01.07.1986 - 30.09.2006**

ORTALAMA AKIMLAR : **Gözlem süresinde 0.246 m3/sn. (16 Yıllık) 2006 Su yılında 0.126 m3/sn.**

ANLIK EN ÇOK VE EN AZ AKIMLAR:

2006 Su yılında anlık encok akım	**:**	**5.32 m3/sn**	**18.08.2006**
2006 Su yılında anlık enaz akım	**:**	**0.022 m3/sn**	**09.07.2006**
Gözlem süresinde anlık encok akım	**:**	**5.70 m3/sn**	**26.06.1999**
Gözlem süresinde anlık enaz akım	**:**	**0.000 m3/sn**	**01.10.1987**

İstasyon için kullanılmış anahtar bulunamadı.

Akımlar 01 Ekim 2005 'den 30 Eylül 2006' a kadar m3/sn olarak

Gün	Ekim	Kasım	Aralık	Ocak	Şubat	Mart	Nisan	Mayıs	Haziran	Temmuz	Ağustos	Eylül
01	0.115	0.115	0.115	0.115	0.115	0.115	0.115	0.150	0.150	0.380	0.065	0.090
02	0.115	0.115	0.115	0.115	0.115	0.115	0.150	0.230	0.150	0.380	0.065	0.090
03	0.115	0.115	0.115	0.115	0.115	0.115	0.190	0.230	0.150	0.380	0.065	0.090
04	0.115	0.150	0.115	0.115	0.115	0.115	0.150	0.230	0.230	0.380	0.090	0.090
05	0.115	0.150	0.115	0.115	0.115	0.115	0.150	0.230	0.380	0.540	0.115	0.090
06	0.115	0.150	0.115	0.115	0.115	0.115	0.150	0.190	0.320	0.150	0.150	0.090
07	0.115	0.150	0.115	0.115	0.115	0.115	0.150	0.190	0.230	0.050	0.190	0.090
08	0.115	0.115	0.115	0.115	0.115	0.115	0.150	0.190	0.230	0.034	0.115	0.090
09	0.115	0.115	0.115	0.115	0.115	0.115	0.150	0.190	0.290	0.022	0.065	0.090
10	0.115	0.115	0.115	0.115	0.115	0.115	0.150	0.190	0.230	0.022	0.065	0.090
11	0.115	0.115	0.115	0.115	0.115	0.115	0.150	0.190	0.230	0.022	0.065	0.090
12	0.115	0.115	0.115	0.115	0.115	0.115	0.150	0.190	0.230	0.022	0.065	0.090
13	0.115	0.115	0.115	0.115	0.115	0.115	0.150	0.190	0.230	0.022	0.065	0.090
14	0.115	0.115	0.115	0.115	0.115	0.115	0.150	0.190	0.190	0.022	0.065	0.090
15	0.115	0.115	0.115	0.115	0.115	0.115	0.150	0.090	0.150	0.022	0.065	0.090
16	0.115	0.115	0.150	0.115	0.115	0.115	0.150	0.050	0.150	0.022	0.065	0.090
17	0.115	0.115	0.150	0.115	0.115	0.115	0.150	0.230	0.090	0.022	0.065	0.090
18	0.115	0.115	0.115	0.115	0.115	0.115	0.150	0.230	0.090	0.022	0.190	0.090
19	0.115	0.115	0.150	0.115	0.115	0.115	0.150	0.190	0.090	0.022	0.320	0.090
20	0.115	0.115	0.115	0.115	0.115	0.115	0.150	0.190	0.090	0.022	0.115	0.090
21	0.115	0.115	0.115	0.115	0.115	0.115	0.150	0.190	0.065	0.050	0.115	0.090
22	0.115	0.115	0.115	0.115	0.115	0.115	0.150	0.190	0.034	0.065	0.090	0.090
23	0.115	0.115	0.115	0.115	0.115	0.115	0.150	0.190	0.034	0.065	0.090	0.115
24	0.115	0.115	0.115	0.115	0.115	0.115	0.150	0.150	0.034	0.065	0.090	0.150
25	0.115	0.115	0.115	0.115	0.115	0.115	0.190	0.150	0.090	0.065	0.230	0.115
26	0.115	0.115	0.115	0.115	0.115	0.115	0.190	0.150	0.090	0.065	0.230	0.115
27	0.115	0.115	0.115	0.115	0.115	0.115	0.150	0.150	0.090	0.065	0.115	0.115
28	0.115	0.115	0.115	0.115	0.115	0.115	0.150	0.150	0.230	0.065	0.090	0.115
29	0.115	0.115	0.115	0.115	-----	0.115	0.150	0.150	0.320	0.065	0.090	0.115
30	0.115	0.115	0.115	0.115	-----	0.115	0.150	0.150	0.380	0.065	0.090	0.115
31	0.115	-----	0.115	0.115	-----	0.115	-----	0.150	-----	0.065	0.090	-----
Maks.	0.150	0.190	0.320	0.190	0.190	0.150	0.230	0.320	5.05	3.90	5.32	0.920
Min.	0.115	0.090	0.115	0.115	0.115	0.115	0.115	0.034	0.034	0.022	0.034	0.065
Ortalama	0.115	0.120	0.118	0.115	0.115	0.115	0.153	0.178	0.176	0.105	0.109	0.098
LT/SN/Km2	2.58	2.68	2.65	2.58	2.58	2.58	3.43	4.00	3.94	2.36	2.45	2.19
AKIM mm.	6.91	6.95	7.11	6.91	6.24	6.91	8.88	10.7	10.2	6.31	6.56	5.69
MİL. M3	0.308	0.310	0.317	0.308	0.278	0.308	0.396	0.478	0.455	0.281	0.292	0.254

SU YILI (2006) YILLIK TOPLAM AKIM 3.99 MİLYON M3 89 MM. 2.8 LT/SN/Km2

16. Konya Kapali Havzasi

D16A149 Bolasan Deriv.Kan. Saraycik

YERİ : **ILGIN ORMANÖZÜ KÖYÜ YOL ÜZERİ.**
31°54'11" Doğu - 38°14'21" Kuzey

YAĞIŞ ALANI : **---- km2** **YAKLAŞIK KOT : 1075 m**

GÖZLEM SÜRESİ : **19.11.1986 - 30.09.2006**

ORTALAMA AKIMLAR : **Gözlem süresinde 0.664 m3/sn. (14 Yıllık) 2006 Su yılında 0.465 m3/sn.**

ANLIK EN ÇOK VE EN AZ AKIMLAR:

2006 Su yılında anlık ençok akım	**:**	**7.30 m3/sn**	**24.04.2006**
2006 Su yılında anlık enaz akım	**:**	**0.000 m3/sn**	**01.10.2005**
Gözlem süresinde anlık ençok akım	**:**	**7.46 m3/sn**	**01.05.2005**
Gözlem süresinde anlık enaz akım	**:**	**0.000 m3/sn**	**01.10.1986**

İstasyon için kullanılmış anahtar bulunamadı.

Akımlar 01 Ekim 2005 'den 30 Eylül 2006' a kadar m3/sn olarak

Gün	Ekim	Kasım	Aralık	Ocak	Şubat	Mart	Nisan	Mayıs	Haziran	Temmuz	Ağustos	Eylül
01	KURU	KURU	0.496	0.408	0.452	1.30	1.40	1.10	0.043	0.029	KURU	KURU
02	KURU	KURU	0.496	0.408	0.320	1.40	1.30	1.20	0.015	0.013	KURU	KURU
03	KURU	KURU	0.652	0.408	0.408	1.60	1.10	1.50	0.013	KURU	KURU	KURU
04	KURU	KURU	0.596	0.408	0.408	1.60	1.10	1.50	0.001	KURU	KURU	KURU
05	KURU	KURU	0.652	0.452	0.408	1.00	1.10	2.44	0.001	KURU	KURU	KURU
06	KURU	KURU	0.652	0.452	0.452	0.830	1.10	2.14	KURU	KURU	KURU	KURU
07	KURU	0.001	0.652	0.408	0.652	0.900	1.10	1.90	KURU	KURU	KURU	KURU
08	KURU	0.104	0.652	0.452	0.160	1.00	1.00	1.96	KURU	KURU	KURU	KURU
09	KURU	0.127	0.596	0.452	0.130	1.00	1.00	2.50	KURU	KURU	KURU	KURU
10	KURU	0.127	0.540	0.452	0.114	0.760	1.20	2.14	KURU	KURU	KURU	KURU
11	KURU	0.127	0.596	0.408	0.250	0.760	1.00	2.02	0.001	KURU	KURU	KURU
12	KURU	0.127	0.540	0.408	0.830	0.760	0.760	1.90	0.036	KURU	KURU	KURU
13	KURU	0.127	0.496	0.408	0.690	0.830	0.550	1.80	0.015	KURU	KURU	KURU
14	KURU	0.104	0.452	0.408	0.430	1.10	0.480	1.70	0.003	KURU	KURU	KURU
15	KURU	0.127	0.452	0.408	0.330	1.10	0.480	1.60	KURU	KURU	KURU	KURU
16	KURU	0.127	0.452	0.408	0.190	1.30	1.20	1.50	KURU	KURU	KURU	KURU
17	KURU	0.127	0.496	0.452	0.220	1.10	0.900	1.70	KURU	KURU	KURU	KURU
18	KURU	0.184	0.452	0.496	0.220	1.00	0.620	1.50	KURU	KURU	KURU	KURU
19	KURU	0.320	0.452	0.452	0.760	1.60	0.330	1.10	KURU	KURU	KURU	KURU
20	KURU	0.320	0.496	0.496	0.830	1.60	0.190	1.20	KURU	KURU	KURU	KURU
21	KURU	0.540	0.452	0.496	1.80	1.50	0.098	1.20	KURU	KURU	KURU	KURU
22	KURU	0.452	0.596	0.496	1.50	1.30	0.114	0.900	KURU	KURU	KURU	KURU
23	KURU	0.364	0.652	0.540	1.20	1.10	0.280	0.760	KURU	KURU	KURU	0.035
24	KURU	0.364	0.652	0.596	1.30	1.50	5.30	0.550	KURU	KURU	KURU	0.035
25	KURU	0.364	0.652	0.596	1.50	1.40	2.68	0.480	KURU	KURU	KURU	0.252
26	KURU	0.408	0.540	0.596	1.60	1.40	0.900	0.280	KURU	KURU	KURU	0.364
27	KURU	0.408	0.408	0.596	1.80	1.30	1.96	0.620	KURU	KURU	KURU	0.364
28	KURU	0.364	0.408	0.496	1.40	1.20	1.50	0.250	KURU	KURU	KURU	0.320
29	KURU	0.496	0.408	0.452	-----	1.20	1.40	0.160	KURU	KURU	KURU	0.364
30	KURU	0.496	0.452	0.452	-----	1.10	1.20	0.114	0.043	KURU	KURU	0.320
31	KURU	-----	0.408	0.452	-----	1.20	-----	0.082	-----	KURU	KURU	-----
Maks.	KURU	0.596	0.708	0.652	2.14	2.08	7.30	2.92	0.082	0.043	KURU	0.452
Min.	KURU	KURU	0.150	0.320	0.019	0.620	0.082	0.066	KURU	KURU	KURU	KURU
Ortalama	KURU	0.210	0.532	0.465	0.727	1.19	1.11	1.28	0.006	0.001	KURU	0.068
LT/SN/Km2	0.000	0.000	0.000	0.000	0.000	0.000	0.000	0.000	0.000	0.000	0.000	0.000
AKIM mm.	0.000	0.000	0.000	0.000	0.000	0.000	0.000	0.000	0.000	0.000	0.000	0.000
MİL. M3	0.000	0.545	1.43	1.25	1.76	3.17	2.88	3.44	0.015	0.004	0.000	0.177

SU YILI (2006) YILLIK TOPLAM AKIM 14.67 MİLYON M3 0 MM. 0.0 LT/SN/Km2

16. Konya Kapali Havzasi

D16A151 Çebisçi S. Argithani

YERİ : **ILGIN ARGITHANI BELDESİ.**
31°43'41" Doğu - 38°18'27" Kuzey

YAĞIŞ ALANI : **181,20 km2** **YAKLAŞIK KOT : 1100 m**

GÖZLEM SÜRESİ : **09.03.1989 - 30.09.2006**

ORTALAMA AKIMLAR : **Gözlem süresinde 0.527 m3/sn. (15 Yıllık) 2006 Su yılında 0.349 m3/sn.**

ANLIK EN ÇOK VE EN AZ AKIMLAR:

2006 Su yılında anlık encok akım	**:**	**4.90**	**m3/sn**	**24.04.2006**
2006 Su yılında anlık enaz akım	**:**	**0.000**	**m3/sn**	**01.10.2005**
Gözlem süresinde anlık encok akım	**:**	**23.0**	**m3/sn**	**29.03.1996**
Gözlem süresinde anlık enaz akım	**:**	**0.000**	**m3/sn**	**01.10.1990**

İstasyon için kullanılmış anahtar bulunamadı.

Akımlar 01 Ekim 2005 'den 30 Eylül 2006' a kadar m3/sn olarak

Gün	Ekim	Kasım	Aralık	Ocak	Şubat	Mart	Nisan	Mayıs	Haziran	Temmuz	Ağustos	Eylül
01	KURU	0.090	0.240	0.330	0.330	0.620	0.954	0.860	0.030	0.090	KURU	KURU
02	KURU	0.090	0.240	0.330	0.420	0.620	0.954	1.24	0.030	0.030	KURU	KURU
03	KURU	0.090	0.240	0.330	0.420	0.620	0.954	2.33	0.020	KURU	KURU	KURU
04	KURU	0.160	0.240	0.330	0.420	0.520	0.954	1.33	KURU	0.090	KURU	KURU
05	KURU	0.240	0.160	0.330	0.420	0.520	0.954	2.15	KURU	0.030	KURU	KURU
06	KURU	0.330	0.160	0.330	0.420	0.520	0.860	1.89	KURU	0.030	KURU	KURU
07	KURU	0.420	0.160	0.330	0.620	0.520	0.860	1.14	KURU	KURU	KURU	KURU
08	KURU	0.520	0.240	0.330	0.760	0.620	0.760	1.14	KURU	KURU	KURU	KURU
09	KURU	0.520	0.240	0.330	0.620	0.760	0.760	1.05	KURU	KURU	KURU	KURU
10	KURU	0.420	0.240	0.420	0.520	0.620	0.860	0.954	KURU	KURU	KURU	KURU
11	KURU	0.330	0.240	0.420	0.760	0.620	0.620	0.860	KURU	KURU	KURU	KURU
12	KURU	0.330	0.240	0.330	1.24	0.620	0.620	0.760	0.030	KURU	KURU	KURU
13	KURU	0.330	0.240	0.330	1.14	0.620	0.520	0.760	0.030	KURU	KURU	KURU
14	KURU	0.240	0.160	0.330	0.954	0.954	0.420	0.620	0.030	KURU	KURU	KURU
15	KURU	0.240	0.160	0.330	0.860	1.33	0.420	0.520	0.030	KURU	KURU	KURU
16	KURU	0.240	0.160	0.330	0.620	1.24	0.420	0.520	0.030	KURU	KURU	KURU
17	0.030	0.240	0.160	0.330	0.760	1.24	0.420	0.520	0.030	KURU	KURU	KURU
18	0.090	0.240	0.240	0.330	0.760	1.24	0.420	0.520	KURU	KURU	KURU	KURU
19	0.090	0.240	0.240	0.330	0.620	1.33	0.330	0.520	KURU	KURU	KURU	KURU
20	0.090	0.240	0.240	0.330	0.760	1.33	0.330	0.520	KURU	KURU	KURU	KURU
21	0.090	0.330	0.240	0.330	0.860	1.24	0.330	0.420	KURU	KURU	KURU	KURU
22	0.090	0.420	0.240	0.330	0.860	1.24	0.240	0.420	KURU	KURU	KURU	KURU
23	0.090	0.420	0.330	0.420	0.860	1.33	0.330	0.330	KURU	KURU	KURU	KURU
24	0.090	0.420	0.420	0.420	0.760	1.42	2.76	0.160	KURU	KURU	KURU	KURU
25	0.090	0.330	0.330	0.420	0.620	1.33	3.09	0.090	KURU	KURU	KURU	KURU
26	0.090	0.240	0.330	0.420	0.620	1.33	1.52	0.090	KURU	KURU	KURU	KURU
27	0.090	0.240	0.330	0.520	0.620	1.24	1.24	0.090	KURU	KURU	KURU	KURU
28	0.090	0.240	0.420	0.520	0.520	1.24	1.14	0.090	KURU	KURU	KURU	KURU
29	0.090	0.240	0.420	0.520	-----	1.14	1.05	0.090	KURU	KURU	KURU	KURU
30	0.090	0.240	0.420	0.520	-----	1.05	0.860	0.090	0.240	KURU	KURU	KURU
31	0.090	-----	0.330	0.330	-----	0.954	-----	0.090	-----	KURU	KURU	-----
Maks.	0.090	0.520	0.420	0.620	1.24	1.42	4.90	3.34	0.330	0.160	KURU	KURU
Min.	KURU	0.090	0.160	0.330	0.330	0.520	0.240	0.090	KURU	KURU	KURU	KURU
Ortalama	0.042	0.289	0.260	0.372	0.684	0.967	0.865	0.715	0.017	0.009	KURU	KURU
LT/SN/Km2	0.230	1.59	1.43	2.05	3.77	5.34	4.77	3.95	0.092	0.048	0.000	0.000
AKIM mm.	0.615	4.13	3.84	5.50	9.13	14.3	12.4	10.6	0.238	0.129	0.000	0.000
MİL. M3	0.111	0.749	0.696	0.996	1.65	2.59	2.24	1.91	0.043	0.023	0.000	0.000

SU YILI (2006) YILLIK TOPLAM AKIM 11.01 MİLYON M3 61 MM. 1.9 LT/SN/Km2

16. Konya Kapali Havzasi

D16A154 Ozan D. Tolca

YERİ : **BEYŞEHİR TOLCA KÖYÜ.**
31°29'35" Doğu - 37°55'3" Kuzey

YAĞIŞ ALANI : **61,27 km2** **YAKLAŞIK KOT : 1199 m**

GÖZLEM SÜRESİ : **01.10.1991 - 30.09.2006**

ORTALAMA AKIMLAR : **Gözlem süresinde 0.097 m3/sn. (15 Yıllık) 2006 Su yılında 0.092 m3/sn.**

ANLIK EN ÇOK VE EN AZ AKIMLAR:

2006 Su yılında anlık ençok akım	**:**	**3.68**	**m3/sn**	**22.03.2006**
2006 Su yılında anlık enaz akım	**:**	**0.000**	**m3/sn**	**01.10.2005**
Gözlem süresinde anlık ençok akım	**:**	**19.8**	**m3/sn**	**28.12.2001**
Gözlem süresinde anlık enaz akım	**:**	**0.000**	**m3/sn**	**01.10.1991**

İstasyon için kullanılmış anahtar bulunamadı.

Akımlar 01 Ekim 2005 'den 30 Eylül 2006' a kadar m3/sn olarak

Gün	Ekim	Kasım	Aralık	Ocak	Şubat	Mart	Nisan	Mayıs	Haziran	Temmuz	Ağustos	Eylül
01	KURU	KURU	0.006	0.018	0.035	0.110	0.140	0.110	KURU	KURU	KURU	KURU
02	KURU	KURU	0.006	0.018	0.035	0.110	0.140	0.140	KURU	KURU	KURU	KURU
03	KURU	KURU	0.006	0.018	0.035	0.110	0.140	0.110	KURU	KURU	KURU	KURU
04	KURU	KURU	0.018	0.018	0.035	0.110	0.140	0.110	KURU	KURU	KURU	KURU
05	KURU	KURU	0.018	0.035	0.035	0.110	0.140	0.110	KURU	KURU	KURU	KURU
06	KURU	KURU	0.006	0.035	0.035	0.110	0.140	0.110	KURU	KURU	KURU	KURU
07	KURU	KURU	0.006	0.035	0.035	0.110	0.140	0.110	KURU	KURU	KURU	KURU
08	KURU	KURU	0.018	0.056	0.035	0.110	0.084	0.110	KURU	KURU	KURU	KURU
09	KURU	KURU	0.006	0.056	0.180	0.220	0.084	0.110	KURU	KURU	KURU	KURU
10	KURU	KURU	0.006	0.056	0.140	0.180	0.084	0.110	KURU	KURU	KURU	KURU
11	KURU	KURU	0.001	0.056	0.350	0.180	0.084	0.110	KURU	KURU	KURU	KURU
12	KURU	KURU	0.001	0.035	0.700	0.140	0.084	0.056	KURU	KURU	KURU	KURU
13	KURU	KURU	0.001	0.035	0.460	0.263	0.056	0.056	KURU	KURU	KURU	KURU
14	KURU	KURU	0.018	0.035	0.263	0.520	0.056	0.056	KURU	KURU	KURU	KURU
15	KURU	0.006	0.018	0.035	0.140	1.31	0.056	0.056	KURU	KURU	KURU	KURU
16	KURU	0.056	0.018	0.056	0.140	2.00	0.035	0.056	KURU	KURU	KURU	KURU
17	KURU	0.006	0.035	0.056	0.140	2.72	0.056	0.056	KURU	KURU	KURU	KURU
18	KURU	0.001	0.035	0.035	0.110	2.60	0.001	0.056	KURU	0.001	KURU	KURU
19	KURU	0.001	0.035	0.035	0.110	2.84	KURU	0.056	KURU	KURU	KURU	KURU
20	KURU	0.001	0.056	0.035	0.110	2.60	KURU	0.084	KURU	0.035	KURU	KURU
21	KURU	0.035	0.056	0.035	0.140	2.48	KURU	0.056	KURU	KURU	KURU	KURU
22	KURU	0.035	0.056	0.035	0.140	0.838	0.001	0.035	KURU	KURU	KURU	KURU
23	KURU	0.035	0.035	0.035	0.110	0.220	0.035	0.035	KURU	KURU	KURU	KURU
24	KURU	0.035	0.035	0.035	0.110	0.220	1.31	0.035	KURU	KURU	KURU	KURU
25	KURU	0.018	0.035	0.035	0.110	0.220	0.405	0.001	KURU	KURU	KURU	KURU
26	KURU	0.018	0.035	0.035	0.110	0.180	0.220	0.001	KURU	KURU	KURU	KURU
27	KURU	0.006	0.035	0.035	0.110	0.180	0.180	KURU	KURU	KURU	KURU	KURU
28	KURU	0.006	0.018	0.035	0.110	0.180	0.110	KURU	KURU	KURU	KURU	KURU
29	KURU	0.006	0.018	0.035	-----	0.180	0.110	KURU	0.001	KURU	KURU	KURU
30	KURU	0.006	0.018	0.035	-----	0.140	0.110	KURU	KURU	KURU	KURU	KURU
31	KURU	-----	0.018	0.035	-----	0.140	-----	KURU	-----	KURU	KURU	-----
Maks.	KURU	0.263	0.056	0.056	0.838	3.68	2.60	0.220	0.018	0.084	KURU	KURU
Min.	KURU	KURU	0.001	0.018	0.018	0.110	KURU	KURU	KURU	KURU	KURU	KURU
Ortalama	KURU	0.009	0.022	0.037	0.145	0.691	0.138	0.062	0.000	0.001	KURU	KURU
LT/SN/Km2	0.000	0.147	0.354	0.602	2.37	11.3	2.25	1.02	0.001	0.019	0.000	0.000
AKIM mm.	0.000	0.382	0.949	1.61	5.73	30.2	5.84	2.73	0.001	0.051	0.000	0.000
MİL. M3	0.000	0.023	0.058	0.099	0.351	1.85	0.358	0.167	0.000	0.003	0.000	0.000

SU YILI (2006) YILLIK TOPLAM AKIM 2.91 MİLYON M3 47 MM. 1.5 LT/SN/Km2

16. Konya Kapali Havzasi

D16A155 Çavusköy D. Kireli

YERİ : **BEYŞEHİR KIRELI BELDESI GIRIŞI YOL ÜSTÜ**
31°32'30" Doğu - 37°55'8" Kuzey

YAĞIŞ ALANI : **51,70 km2** **YAKLAŞIK KOT : 1225 m**

GÖZLEM SÜRESİ : **01.10.1991 - 30.09.2006**

ORTALAMA AKIMLAR : **Gözlem süresinde 0.219 m3/sn. (15 Yıllık) 2006 Su yılında 0.156 m3/sn.**

ANLIK EN ÇOK VE EN AZ AKIMLAR:

2006 Su yılında anlık ençok akım	**:**	**16.6**	**m3/sn**	**24.04.2006**
2006 Su yılında anlık enaz akım	**:**	**0.000**	**m3/sn**	**01.10.2005**
Gözlem süresinde anlık ençok akım	**:**	**51.8**	**m3/sn**	**30.01.1999**
Gözlem süresinde anlık enaz akım	**:**	**0.000**	**m3/sn**	**01.10.1993**

İstasyon için kullanılmış anahtar bulunamadı.

Akımlar 01 Ekim 2005 'den 30 Eylül 2006' a kadar m3/sn olarak

Gün	Ekim	Kasım	Aralık	Ocak	Şubat	Mart	Nisan	Mayıs	Haziran	Temmuz	Ağustos	Eylül
01	KURU	KURU	0.001	0.160	0.083	0.400	0.277	0.160	KURU	KURU	KURU	KURU
02	KURU	KURU	0.006	0.160	0.083	0.475	0.277	0.338	KURU	KURU	KURU	KURU
03	KURU	KURU	0.006	0.160	0.115	0.475	0.215	0.400	KURU	KURU	KURU	KURU
04	KURU	KURU	0.006	0.115	0.160	0.400	0.215	0.475	KURU	KURU	KURU	KURU
05	KURU	KURU	0.006	0.115	0.160	0.338	0.277	0.338	KURU	KURU	KURU	KURU
06	KURU	KURU	0.006	0.115	0.215	0.277	0.277	0.338	KURU	KURU	KURU	KURU
07	KURU	KURU	0.001	0.115	0.215	0.338	0.215	0.277	KURU	KURU	KURU	KURU
08	KURU	KURU	0.001	0.160	0.277	0.338	0.160	0.160	KURU	KURU	KURU	KURU
09	KURU	KURU	0.006	0.160	0.277	0.400	0.160	0.083	KURU	KURU	KURU	KURU
10	KURU	KURU	0.006	0.215	0.400	0.400	0.115	0.042	KURU	KURU	KURU	KURU
11	KURU	KURU	0.006	0.215	0.820	0.400	0.115	0.014	KURU	KURU	KURU	KURU
12	KURU	KURU	0.006	0.160	0.910	0.400	0.115	0.006	KURU	KURU	KURU	KURU
13	KURU	KURU	0.006	0.160	0.550	0.640	0.115	KURU	KURU	KURU	KURU	KURU
14	KURU	KURU	0.042	0.115	0.338	1.00	0.115	KURU	KURU	KURU	KURU	KURU
15	KURU	KURU	0.042	0.115	0.338	1.00	0.063	KURU	KURU	KURU	KURU	KURU
16	KURU	KURU	0.042	0.063	0.338	0.910	0.063	KURU	KURU	KURU	KURU	KURU
17	KURU	KURU	0.042	0.083	0.338	0.730	0.042	KURU	KURU	KURU	KURU	KURU
18	KURU	KURU	0.042	0.063	0.338	0.730	0.025	KURU	KURU	KURU	KURU	KURU
19	KURU	KURU	0.042	0.063	0.277	0.820	KURU	KURU	KURU	KURU	KURU	KURU
20	KURU	KURU	0.042	0.042	0.277	0.820	KURU	0.001	KURU	KURU	KURU	KURU
21	KURU	0.001	0.063	0.042	0.277	0.640	KURU	0.014	KURU	KURU	KURU	KURU
22	KURU	0.025	0.063	0.063	0.215	0.550	KURU	0.014	KURU	KURU	KURU	KURU
23	KURU	0.042	0.063	0.063	0.215	0.475	0.550	0.006	KURU	KURU	KURU	KURU
24	KURU	0.025	0.063	0.063	0.215	0.475	11.4	0.001	KURU	KURU	KURU	KURU
25	KURU	0.025	0.083	0.083	0.338	0.475	6.97	KURU	KURU	KURU	KURU	KURU
26	KURU	0.025	0.083	0.083	0.338	0.400	1.56	KURU	KURU	KURU	KURU	KURU
27	KURU	0.014	0.115	0.083	0.475	0.400	0.475	KURU	KURU	KURU	KURU	KURU
28	KURU	0.006	0.115	0.083	0.475	0.338	0.215	KURU	KURU	KURU	KURU	KURU
29	KURU	0.006	0.160	0.063	-----	0.338	0.115	KURU	KURU	KURU	KURU	KURU
30	KURU	0.001	0.160	0.063	-----	0.277	0.115	KURU	KURU	KURU	KURU	KURU
31	KURU	-----	0.160	0.083	-----	0.277	-----	KURU	-----	KURU	KURU	-----
Maks.	KURU	0.042	0.160	0.215	1.00	1.56	16.6	0.475	KURU	KURU	KURU	KURU
Min.	KURU	KURU	0.001	0.042	0.083	0.215	KURU	KURU	KURU	KURU	KURU	KURU
Ortalama	KURU	0.006	0.048	0.107	0.323	0.514	0.808	0.086	KURU	KURU	KURU	KURU
LT/SN/Km2	0.000	0.110	0.927	2.08	6.26	9.94	15.6	1.66	0.000	0.000	0.000	0.000
AKIM mm.	0.000	0.284	2.48	5.56	15.1	26.6	40.5	4.46	0.000	0.000	0.000	0.000
MİL. M3	0.000	0.015	0.128	0.287	0.783	1.38	2.09	0.230	0.000	0.000	0.000	0.000

SU YILI (2006) YILLIK TOPLAM AKIM 4.91 MİLYON M3 95 MM. 3.0 LT/SN/Km2

16. Konya Kapali Havzasi

D16A158 Hizar D. Gölyaka

YERİ : **BEYŞEHİR GÖLYAKA**
31°26'18" Doğu - 37°43'35" Kuzey

YAĞIŞ ALANI : **155,00 km2** **YAKLAŞIK KOT : 1125 m**

GÖZLEM SÜRESİ : **01.10.1991 - 30.09.2006**

ORTALAMA AKIMLAR : **Gözlem süresinde 0.496 m3/sn. (14 Yıllık) 2006 Su yılında 0.340 m3/sn.**

ANLIK EN ÇOK VE EN AZ AKIMLAR:

2006 Su yılında anlık ençok akım	**:**	**5.00**	**m3/sn**	**11.02.2006**
2006 Su yılında anlık enaz akım	**:**	**0.000**	**m3/sn**	**01.10.2005**
Gözlem süresinde anlık ençok akım	**:**	**29.5**	**m3/sn**	**25.04.1997**
Gözlem süresinde anlık enaz akım	**:**	**0.000**	**m3/sn**	**31.10.2000**

İstasyon için kullanılmış anahtar bulunamadı.

Akımlar 01 Ekim 2005 'den 30 Eylül 2006' a kadar m3/sn olarak

Gün	Ekim	Kasım	Aralık	Ocak	Şubat	Mart	Nisan	Mayıs	Haziran	Temmuz	Ağustos	Eylül
01	KURU	KURU	KURU	KURU	KURU	0.796	1.60	1.30	0.096	0.050	0.016	KURU
02	KURU	KURU	KURU	KURU	KURU	0.796	1.60	1.75	0.096	0.050	0.016	KURU
03	KURU	KURU	KURU	KURU	KURU	1.03	1.45	1.45	0.096	0.016	0.016	KURU
04	KURU	KURU	KURU	KURU	KURU	1.15	1.30	1.30	0.096	0.016	0.016	KURU
05	KURU	KURU	KURU	KURU	KURU	0.914	1.30	1.30	0.050	0.016	0.016	KURU
06	KURU	KURU	KURU	KURU	KURU	0.796	1.15	1.15	0.096	0.016	0.001	KURU
07	KURU	KURU	KURU	KURU	KURU	0.796	1.45	1.15	0.096	0.016	0.001	KURU
08	KURU	KURU	KURU	KURU	KURU	1.30	1.75	1.15	0.050	0.016	0.001	KURU
09	KURU	KURU	KURU	KURU	KURU	1.03	1.75	1.03	0.050	0.016	0.001	KURU
10	KURU	KURU	KURU	KURU	KURU	0.678	1.45	0.914	0.096	0.016	0.001	KURU
11	KURU	KURU	KURU	KURU	0.914	0.560	1.45	1.03	0.096	0.016	0.001	KURU
12	KURU	KURU	KURU	KURU	0.678	0.560	1.75	1.15	0.050	0.016	KURU	KURU
13	KURU	KURU	KURU	KURU	1.03	0.796	2.26	1.15	0.096	0.016	KURU	KURU
14	KURU	KURU	KURU	KURU	0.370	1.15	2.44	1.30	0.096	0.016	KURU	KURU
15	KURU	KURU	KURU	KURU	0.215	1.15	2.44	1.15	0.152	0.016	KURU	KURU
16	KURU	KURU	KURU	KURU	0.096	1.15	2.08	1.03	0.152	0.016	KURU	KURU
17	KURU	KURU	KURU	KURU	0.050	1.15	1.90	0.678	0.096	0.016	KURU	KURU
18	KURU	KURU	KURU	KURU	0.096	1.03	1.60	0.370	0.096	0.016	KURU	KURU
19	KURU	KURU	0.560	KURU	0.050	1.03	1.45	0.152	0.050	0.016	KURU	KURU
20	KURU	KURU	0.796	KURU	0.096	0.914	1.75	0.215	0.050	0.016	KURU	KURU
21	KURU	KURU	KURU	KURU	0.152	0.914	1.60	0.152	0.050	0.016	KURU	KURU
22	KURU	KURU	KURU	KURU	0.215	1.15	1.75	0.460	0.050	0.016	KURU	KURU
23	KURU	KURU	KURU	KURU	0.290	1.60	1.90	0.096	0.050	0.016	KURU	KURU
24	KURU	KURU	KURU	KURU	0.370	1.90	2.80	0.460	0.050	0.016	KURU	KURU
25	KURU	KURU	KURU	KURU	0.678	2.44	2.44	0.370	0.016	0.016	KURU	KURU
26	KURU	KURU	KURU	KURU	0.796	1.75	1.75	0.152	0.016	0.016	KURU	KURU
27	KURU	KURU	KURU	KURU	1.90	1.45	1.45	0.096	0.016	0.016	KURU	KURU
28	KURU	KURU	KURU	KURU	0.914	1.60	1.30	0.096	0.050	0.016	KURU	KURU
29	KURU	KURU	KURU	KURU	-----	1.45	1.30	0.152	0.050	0.016	KURU	KURU
30	KURU	KURU	KURU	KURU	-----	1.60	1.30	0.152	0.016	0.016	KURU	KURU
31	KURU	-----	KURU	KURU	-----	1.75	-----	0.096	-----	0.016	KURU	-----
Maks.	KURU	KURU	3.75	KURU	5.00	2.99	3.37	1.90	0.215	0.096	0.016	KURU
Min.	KURU	KURU	KURU	KURU	KURU	0.460	1.15	0.096	0.016	0.001	KURU	KURU
Ortalama	KURU	KURU	0.044	KURU	0.318	1.17	1.72	0.742	0.071	0.018	0.003	KURU
LT/SN/Km2	0.000	0.000	0.282	0.000	2.05	7.57	11.1	4.79	0.456	0.117	0.018	0.000
AKIM mm.	0.000	0.000	0.756	0.000	4.97	20.3	28.7	12.8	1.18	0.314	0.048	0.000
MİL. M3	0.000	0.000	0.117	0.000	0.770	3.14	4.45	1.99	0.183	0.049	0.007	0.000

SU YILI (2006) YILLIK TOPLAM AKIM 10.71 MİLYON M3 69 MM. 2.2 LT/SN/Km2

16. Konya Kapali Havzasi

D16A161 Akçardak D. Melikli

YERİ : **33°47'25" Doğu - 37°10'52" Kuzey**

YAĞIŞ ALANI : **---- km2** **YAKLAŞIK KOT : 1420 m**

GÖZLEM SÜRESİ : **01.10.1997 - 30.09.2006**

ORTALAMA AKIMLAR : **Gözlem süresinde 0.527 m3/sn. (8 Yıllık) 2006 Su yılında 0.171 m3/sn.**

ANLIK EN ÇOK VE EN AZ AKIMLAR:

2006 Su yılında anlık ençok akım	**:**	**2.44**	**m3/sn**	**10.04.2006**
2006 Su yılında anlık enaz akım	**:**	**0.000**	**m3/sn**	**01.10.2005**
Gözlem süresinde anlık ençok akım	**:**	**43.3**	**m3/sn**	**08.09.2002**
Gözlem süresinde anlık enaz akım	**:**	**0.000**	**m3/sn**	**01.10.1997**

İstasyon için kullanılmış anahtar bulunamadı.

Akımlar 01 Ekim 2005 'den 30 Eylül 2006' a kadar m3/sn olarak

Gün	Ekim	Kasım	Aralık	Ocak	Şubat	Mart	Nisan	Mayıs	Haziran	Temmuz	Ağustos	Eylül
01	KURU	0.013	KURU	0.013	KURU	0.230	1.74	0.460	KURU	KURU	KURU	KURU
02	KURU	KURU	KURU	0.013	KURU	0.390	1.74	0.380	KURU	KURU	KURU	KURU
03	KURU	KURU	KURU	KURU	KURU	0.470	1.60	0.380	KURU	KURU	KURU	KURU
04	KURU	0.013	KURU	KURU	KURU	0.462	1.48	0.290	KURU	KURU	KURU	KURU
05	KURU	0.013	KURU	KURU	KURU	0.548	1.23	0.290	KURU	KURU	KURU	KURU
06	KURU	0.013	KURU	KURU	KURU	0.462	1.10	0.380	KURU	KURU	KURU	KURU
07	KURU	0.013	KURU	KURU	0.013	0.634	1.23	0.380	KURU	KURU	KURU	KURU
08	KURU	0.013	KURU	KURU	0.013	0.836	1.35	0.290	KURU	KURU	KURU	KURU
09	KURU	0.013	KURU	KURU	0.013	0.720	1.10	0.290	KURU	KURU	KURU	KURU
10	KURU	0.013	KURU	KURU	0.013	0.548	1.74	0.290	KURU	KURU	KURU	KURU
11	KURU	0.013	KURU	KURU	0.013	0.462	1.35	0.290	KURU	KURU	KURU	KURU
12	KURU	0.013	KURU	KURU	0.013	0.376	1.35	0.290	KURU	KURU	KURU	KURU
13	KURU	0.013	KURU	KURU	0.013	0.376	1.23	0.290	KURU	KURU	KURU	KURU
14	KURU	0.013	KURU	KURU	0.013	0.462	1.10	0.290	KURU	KURU	KURU	KURU
15	KURU	0.013	0.013	KURU	0.013	0.548	0.980	0.290	KURU	KURU	KURU	KURU
16	KURU	0.013	0.013	KURU	0.013	0.462	1.10	0.290	KURU	KURU	KURU	KURU
17	KURU	0.013	0.013	KURU	0.013	0.462	0.980	0.220	KURU	KURU	KURU	KURU
18	KURU	0.013	0.013	KURU	0.013	0.462	0.980	0.220	KURU	KURU	KURU	KURU
19	KURU	0.013	0.013	KURU	0.013	0.548	0.876	0.160	KURU	KURU	KURU	KURU
20	KURU	0.013	0.013	KURU	0.013	0.548	0.668	0.160	KURU	KURU	KURU	KURU
21	KURU	0.013	0.013	KURU	0.013	0.548	0.668	0.160	KURU	KURU	KURU	KURU
22	KURU	0.013	0.013	KURU	0.013	0.634	0.564	0.110	KURU	KURU	KURU	KURU
23	KURU	0.013	0.013	KURU	0.013	1.07	0.564	0.110	KURU	KURU	KURU	KURU
24	KURU	0.013	0.013	KURU	0.013	1.72	0.564	0.110	KURU	KURU	KURU	KURU
25	KURU	0.013	0.013	KURU	0.013	1.86	0.564	0.073	KURU	KURU	KURU	KURU
26	KURU	0.013	0.013	KURU	0.013	1.48	0.564	0.037	KURU	KURU	KURU	KURU
27	KURU	0.013	0.013	KURU	0.055	1.35	0.460	0.015	KURU	KURU	KURU	KURU
28	KURU	KURU	0.013	KURU	0.160	1.35	0.460	KURU	KURU	KURU	KURU	KURU
29	KURU	KURU	0.013	KURU	-----	1.48	0.460	KURU	KURU	KURU	KURU	KURU
30	KURU	KURU	0.013	KURU	-----	1.35	0.460	KURU	KURU	KURU	KURU	KURU
31	0.013	-----	0.013	KURU	-----	1.74	-----	KURU	-----	KURU	KURU	-----
Maks.	0.013	0.160	0.013	0.013	0.680	1.86	2.44	0.460	KURU	KURU	KURU	KURU
Min.	KURU	KURU	KURU	KURU	KURU	0.160	0.460	KURU	KURU	KURU	KURU	KURU
Ortalama	0.000	0.011	0.007	0.001	0.017	0.793	1.01	0.211	KURU	KURU	KURU	KURU
LT/SN/Km2	0.000	0.000	0.000	0.000	0.000	0.000	0.000	0.000	0.000	0.000	0.000	0.000
AKIM mm.	0.000	0.000	0.000	0.000	0.000	0.000	0.000	0.000	0.000	0.000	0.000	0.000
MİL. M3	0.001	0.028	0.019	0.002	0.041	2.12	2.61	0.565	0.000	0.000	0.000	0.000

SU YILI (2006) YILLIK TOPLAM AKIM 5.39 MİLYON M3 0 MM. 0.0 LT/SN/Km2

16. Konya Kapali Havzasi

D16A163 Ana Bosaltim Kan. Tatlikuyu

YERİ : **33°49'37" Doğu - 37°34'25" Kuzey**

YAĞIŞ ALANI : **---- km2** **YAKLAŞIK KOT : 1002 m**

GÖZLEM SÜRESİ : **01.10.1997 - 30.09.2006**

ORTALAMA AKIMLAR : **Gözlem süresinde 0.527 m3/sn. (6 Yıllık) 2006 Su yılında 0.308 m3/sn.**

ANLIK EN ÇOK VE EN AZ AKIMLAR:

2006 Su yılında anlık ençok akım	**:**	**2.97**	**m3/sn**	**21.01.2006**
2006 Su yılında anlık enaz akım	**:**	**0.000**	**m3/sn**	**04.04.2006**
Gözlem süresinde anlık ençok akım	**:**	**4.04**	**m3/sn**	**25.02.2000**
Gözlem süresinde anlık enaz akım	**:**	**0.000**	**m3/sn**	**01.10.1997**

İstasyon için kullanılmış anahtar bulunamadı.

Akımlar 01 Ekim 2005 'den 30 Eylül 2006' a kadar m3/sn olarak

Gün	Ekim	Kasım	Aralık	Ocak	Şubat	Mart	Nisan	Mayıs	Haziran	Temmuz	Ağustos	Eylül
01	0.046	0.120	0.255	1.16	1.89	0.490	0.080	0.230	KURU	KURU	KURU	KURU
02	0.046	0.120	0.255	1.21	1.89	0.490	0.080	0.155	0.155	KURU	KURU	KURU
03	0.046	0.120	0.210	1.21	1.83	0.490	0.080	0.155	0.370	KURU	KURU	KURU
04	0.046	0.165	0.210	1.21	1.83	0.490	KURU	0.155	0.300	KURU	KURU	KURU
05	0.046	0.165	0.165	1.21	1.83	0.490	KURU	0.080	0.230	KURU	KURU	KURU
06	0.046	0.165	0.165	1.21	2.04	0.490	KURU	KURU	0.155	0.080	KURU	KURU
07	0.046	0.165	0.165	1.21	1.53	0.490	KURU	0.080	0.080	0.155	KURU	KURU
08	0.046	0.165	0.120	1.21	1.53	0.490	KURU	0.155	KURU	0.155	KURU	KURU
09	0.046	0.165	0.120	1.21	1.26	0.490	KURU	0.230	KURU	0.155	KURU	KURU
10	0.046	0.120	0.120	1.21	0.610	0.670	KURU	0.230	KURU	0.080	KURU	0.080
11	0.046	0.165	0.120	1.21	0.550	0.730	KURU	0.230	KURU	0.155	KURU	0.080
12	0.046	0.120	0.120	1.21	0.430	0.670	KURU	0.080	KURU	0.155	KURU	KURU
13	0.046	0.120	0.120	1.21	0.430	0.670	KURU	KURU	KURU	0.080	KURU	KURU
14	0.082	0.165	0.120	1.21	0.430	0.610	KURU	KURU	KURU	0.080	KURU	KURU
15	0.082	0.210	0.120	1.21	0.430	0.610	KURU	KURU	KURU	0.155	KURU	KURU
16	0.082	0.210	0.120	1.48	0.550	0.670	KURU	KURU	KURU	0.155	KURU	KURU
17	0.082	0.210	0.120	1.32	1.00	0.670	KURU	KURU	KURU	0.155	KURU	KURU
18	0.082	0.210	0.120	0.430	0.370	0.610	KURU	KURU	KURU	0.080	KURU	KURU
19	0.082	0.210	0.120	0.370	0.370	0.550	KURU	0.080	KURU	0.080	KURU	KURU
20	0.082	0.165	0.165	0.490	0.370	0.490	KURU	0.080	KURU	0.080	KURU	KURU
21	0.082	0.255	0.165	2.12	0.370	0.430	KURU	KURU	KURU	KURU	0.080	KURU
22	0.120	0.210	0.255	2.25	0.490	0.370	KURU	KURU	KURU	KURU	0.080	KURU
23	0.120	0.210	0.300	2.08	0.490	0.300	KURU	KURU	KURU	KURU	0.080	KURU
24	0.120	0.210	1.53	1.94	0.490	0.300	KURU	KURU	KURU	KURU	0.080	KURU
25	0.120	0.255	1.72	1.89	0.490	0.300	KURU	KURU	KURU	KURU	KURU	KURU
26	0.120	0.255	1.62	1.89	0.490	0.230	KURU	0.080	KURU	KURU	KURU	KURU
27	0.120	0.210	1.62	1.89	0.490	0.230	KURU	0.080	KURU	KURU	KURU	KURU
28	0.120	0.210	1.58	1.89	0.490	0.230	KURU	0.080	KURU	KURU	KURU	KURU
29	0.120	0.210	1.37	1.89	-----	0.155	KURU	KURU	KURU	KURU	KURU	KURU
30	0.120	0.210	1.21	1.89	-----	0.080	KURU	KURU	KURU	KURU	KURU	KURU
31	0.120	-----	1.16	1.89	-----	0.080	-----	KURU	-----	KURU	KURU	-----
Maks.	0.165	0.300	2.20	2.97	2.65	1.48	0.300	0.300	0.670	2.40	0.155	0.490
Min.	0.046	0.120	0.120	0.300	0.230	0.080	KURU	KURU	KURU	KURU	KURU	KURU
Ortalama	0.079	0.183	0.502	1.41	0.892	0.454	0.008	0.070	0.043	0.058	0.010	0.005
LT/SN/Km2	0.000	0.000	0.000	0.000	0.000	0.000	0.000	0.000	0.000	0.000	0.000	0.000
AKIM mm.	0.000	0.000	0.000	0.000	0.000	0.000	0.000	0.000	0.000	0.000	0.000	0.000
MİL. M3	0.212	0.474	1.34	3.79	2.16	1.22	0.021	0.188	0.111	0.156	0.028	0.014

SU YILI (2006) YILLIK TOPLAM AKIM 9.71 MİLYON M3 0 MM. 0.0 LT/SN/Km2

16. Konya Kapali Havzasi

D16A166 Çarsamba S. Pinarcik

YERİ : **BOZKIR PINARCIK KÖYÜ**
32°16'49" Doğu - 37°15'47" Kuzey

YAĞIŞ ALANI : **343,00 km2** **YAKLAŞIK KOT : 1125 m**

GÖZLEM SÜRESİ : **01.10.1998 - 30.09.2006**

ORTALAMA AKIMLAR : **Gözlem süresinde 2.744 m3/sn. (6 Yıllık) 2006 Su yılında 2.007 m3/sn.**

ANLIK EN ÇOK VE EN AZ AKIMLAR:

2006 Su yılında anlık ençok akım	**:**	**24.6**	**m3/sn**	**16.04.2006**
2006 Su yılında anlık enaz akım	**:**	**0.000**	**m3/sn**	**01.10.2005**
Gözlem süresinde anlık ençok akım	**:**	**64.5**	**m3/sn**	**28.12.2001**
Gözlem süresinde anlık enaz akım	**:**	**0.000**	**m3/sn**	**01.10.1999**

50. Anahtar Eğrisi (Seviyeler cm olarak)

Seviye	Akım	Seviye	Akım	Seviye	Akım	Seviye	Akım
61	0.050	160	7.5	250	26.0	300	40.0
80	0.338	180	10.8	260	28.8	310	42.8
100	1.2	200	14.8	270	31.6	320	45.6
120	2.6	220	19.0	280	34.4	330	48.7
140	4.8	240	23.6	290	37.2	336	50.7

Akımlar 01 Ekim 2005 'den 30 Eylül 2006' a kadar m3/sn olarak

Gün	Ekim	Kasım	Aralık	Ocak	Şubat	Mart	Nisan	Mayıs	Haziran	Temmuz	Ağustos	Eylül
01	KURU	KURU	0.580	0.660	1.06	3.14	11.1	5.08	1.35	0.568	KURU	KURU
02	KURU	KURU	0.500	0.620	1.06	3.76	12.2	4.94	1.30	0.474	KURU	KURU
03	KURU	KURU	0.500	0.620	1.06	4.15	10.8	4.94	1.20	0.427	KURU	KURU
04	KURU	KURU	0.500	0.580	1.02	7.72	10.0	4.80	1.15	0.427	KURU	KURU
05	KURU	KURU	0.500	0.580	1.06	7.15	8.86	4.54	1.15	0.427	KURU	KURU
06	KURU	KURU	0.476	0.580	1.18	6.20	8.67	4.41	1.05	0.380	KURU	KURU
07	KURU	KURU	0.428	0.620	2.25	6.06	8.86	4.15	1.05	0.427	KURU	KURU
08	KURU	KURU	0.452	0.780	2.46	6.06	9.24	4.02	1.00	0.308	KURU	KURU
09	KURU	0.010	0.428	0.780	2.04	5.50	9.05	3.89	0.950	0.272	KURU	KURU
10	KURU	0.012	0.428	0.820	1.97	4.54	8.48	3.76	1.00	0.272	KURU	KURU
11	KURU	0.012	0.380	0.860	2.46	4.02	8.10	3.50	0.900	0.272	KURU	KURU
12	KURU	0.033	0.380	0.860	3.32	4.02	8.10	3.42	0.850	0.218	KURU	KURU
13	KURU	0.053	0.380	0.860	3.41	5.22	8.29	3.34	0.803	0.200	KURU	KURU
14	KURU	0.105	0.356	0.900	2.78	5.92	8.67	3.18	0.803	0.200	KURU	KURU
15	KURU	0.094	0.356	0.900	2.39	5.92	9.05	3.10	0.803	0.200	KURU	KURU
16	KURU	0.084	0.332	0.860	2.11	5.92	18.4	3.02	0.803	0.200	KURU	KURU
17	KURU	0.094	0.332	0.860	1.90	5.50	15.6	3.02	0.709	0.187	KURU	KURU
18	KURU	0.476	0.500	0.860	1.78	5.36	11.7	2.86	0.662	0.135	KURU	KURU
19	KURU	0.780	0.980	0.860	1.84	5.22	10.6	2.78	0.615	0.064	KURU	KURU
20	KURU	1.14	0.980	1.84	1.97	5.36	9.81	2.63	0.521	0.046	KURU	KURU
21	KURU	1.18	0.820	1.54	2.11	5.36	9.24	2.56	0.521	0.022	KURU	KURU
22	KURU	0.940	0.780	1.30	2.25	6.06	8.67	2.42	0.521	0.083	KURU	KURU
23	KURU	0.740	0.780	1.30	2.60	7.53	8.48	2.28	0.521	0.064	KURU	KURU
24	KURU	0.660	0.740	1.42	3.05	11.1	8.29	2.21	0.521	0.064	KURU	KURU
25	KURU	0.540	0.740	1.48	3.41	11.7	7.53	2.00	0.380	0.040	KURU	KURU
26	KURU	0.476	0.740	1.36	3.89	10.2	6.77	1.81	0.362	KURU	KURU	KURU
27	KURU	0.500	0.700	1.26	3.23	9.62	6.20	1.68	0.568	KURU	KURU	KURU
28	KURU	0.540	0.700	1.18	3.05	9.43	5.92	1.55	0.521	KURU	KURU	KURU
29	KURU	0.580	0.700	1.10	-----	9.62	5.64	1.48	0.568	KURU	KURU	KURU
30	KURU	0.620	0.660	1.10	-----	9.81	5.50	1.42	0.615	KURU	KURU	KURU
31	KURU	-----	0.660	1.10	-----	11.0	-----	1.42	-----	KURU	KURU	-----
Maks.	KURU	1.36	1.22	2.53	5.50	14.3	24.6	5.50	1.61	0.756	KURU	KURU
Min.	KURU	KURU	0.332	0.540	1.02	3.14	5.36	1.30	0.272	KURU	KURU	KURU
Ortalama	KURU	0.322	0.574	0.982	2.24	6.72	9.26	3.10	0.792	0.193	KURU	KURU
LT/SN/Km2	0.000	0.940	1.67	2.86	6.53	19.6	27.0	9.05	2.31	0.562	0.000	0.000
AKIM mm.	0.000	2.44	4.48	7.67	15.8	52.4	70.0	24.2	5.99	1.51	0.000	0.000
MİL. M3	0.000	0.835	1.54	2.63	5.42	18.0	24.0	8.31	2.05	0.516	0.000	0.000

SU YILI (2006) YILLIK TOPLAM AKIM 63.30 MİLYON M3 185 MM. 5.9 LT/SN/Km2

16. Konya Kapali Havzasi

D16A168 Biçakçi D. Sadiklar

YERİ : **KONYA SADIKLAR KÖYÜ**
32°16'27" Doğu - 37°32'24" Kuzey

YAĞIŞ ALANI : **57,00 km2** **YAKLAŞIK KOT : 1167 m**

GÖZLEM SÜRESİ : **01.10.1999 - 30.09.2006**

ORTALAMA AKIMLAR : **Gözlem süresinde 0.224 m3/sn. (7 Yıllık) 2006 Su yılında 0.196 m3/sn.**

ANLIK EN ÇOK VE EN AZ AKIMLAR:

2006 Su yılında anlık ençok akım	**:**	**9.00**	**m3/sn**	**15.04.2006**
2006 Su yılında anlık enaz akım	**:**	**0.001**	**m3/sn**	**09.08.2006**
Gözlem süresinde anlık ençok akım	**:**	**14.8**	**m3/sn**	**06.09.2002**
Gözlem süresinde anlık enaz akım	**:**	**0.000**	**m3/sn**	**01.10.1999**

İstasyon için kullanılmış anahtar bulunamadı.

Akımlar 01 Ekim 2005 'den 30 Eylül 2006' a kadar m3/sn olarak

Gün	Ekim	Kasım	Aralık	Ocak	Şubat	Mart	Nisan	Mayıs	Haziran	Temmuz	Ağustos	Eylül
01	0.053	0.094	0.094	0.108	1.16	0.368	0.590	0.128	0.045	0.057	0.011	0.029
02	0.053	0.094	0.081	0.142	1.16	0.368	0.590	0.182	0.045	0.036	0.011	0.081
03	0.067	0.094	0.081	0.142	0.635	0.368	0.545	0.275	0.036	0.045	0.007	0.032
04	0.081	0.094	0.081	0.108	0.368	0.456	0.545	0.200	0.036	0.068	0.016	0.025
05	0.081	0.211	0.081	0.094	0.280	0.368	0.500	0.182	0.029	0.045	0.016	0.018
06	0.081	0.545	0.081	0.108	0.456	0.280	0.456	0.164	0.022	0.036	0.011	0.018
07	0.081	0.590	0.081	0.142	1.28	0.280	0.500	0.164	0.011	0.022	0.007	0.013
08	0.067	0.590	0.094	0.142	0.412	0.280	0.545	0.146	0.007	0.022	0.004	0.013
09	0.067	0.500	0.094	0.142	0.368	0.280	0.545	0.200	0.007	0.016	0.001	0.013
10	0.067	0.280	0.094	0.142	0.412	0.246	0.500	0.200	0.016	0.016	0.004	0.009
11	0.067	0.177	0.094	0.108	0.800	0.177	0.456	0.128	0.011	0.022	0.007	0.013
12	0.081	0.177	0.094	0.094	0.920	0.142	0.500	0.110	0.016	0.029	0.016	0.013
13	0.081	0.108	0.094	0.094	0.635	0.280	0.545	0.110	0.011	0.022	0.016	0.013
14	0.081	0.081	0.094	0.094	0.456	0.412	0.635	0.092	0.016	0.016	0.007	0.006
15	0.081	0.081	0.094	0.094	0.368	0.500	1.28	0.092	0.011	0.016	0.011	0.009
16	0.177	0.067	0.094	0.094	0.368	0.456	1.50	0.092	0.016	0.016	0.011	0.009
17	0.280	0.053	0.094	0.211	0.368	0.456	0.620	0.110	0.022	0.022	0.007	0.006
18	0.142	0.053	0.094	0.211	0.324	0.456	0.440	0.110	0.016	0.016	0.016	0.009
19	0.324	0.067	0.142	0.108	0.500	0.500	0.367	0.092	0.016	0.011	0.080	0.009
20	0.246	0.142	0.142	0.500	0.545	0.500	0.333	0.092	0.016	0.022	0.036	0.013
21	0.142	0.368	0.108	0.590	0.635	0.456	0.275	0.080	0.016	0.022	0.022	0.032
22	0.108	0.246	0.094	0.590	0.590	0.456	0.225	0.080	0.011	0.029	0.016	0.043
23	0.108	0.177	0.094	0.500	0.545	0.456	0.225	0.068	0.016	0.022	0.007	0.054
24	0.108	0.142	0.094	0.368	0.500	0.635	0.275	0.057	0.022	0.022	0.004	0.054
25	0.094	0.108	0.280	0.280	0.500	0.590	0.182	0.068	0.029	0.016	0.007	0.065
26	0.094	0.108	0.500	0.280	0.500	0.545	0.164	0.057	0.036	0.016	0.036	0.054
27	0.094	0.108	0.456	0.246	0.500	0.500	0.146	0.057	0.029	0.016	0.029	0.054
28	0.094	0.108	0.280	0.412	0.412	0.456	0.146	0.068	0.029	0.016	0.016	0.032
29	0.094	0.108	0.142	0.680	-----	0.456	0.146	0.045	0.080	0.022	0.007	0.054
30	0.094	0.108	0.142	1.16	-----	0.456	0.146	0.057	0.080	0.016	0.007	0.054
31	0.094	-----	0.142	1.16	-----	0.635	-----	0.057	-----	0.011	0.016	-----
Maks.	0.545	1.16	0.635	1.16	2.44	0.920	9.00	2.20	1.60	0.164	0.250	0.570
Min.	0.053	0.053	0.040	0.094	0.142	0.108	0.092	0.036	0.004	0.011	0.001	0.001
Ortalama	0.109	0.189	0.136	0.295	0.571	0.413	0.464	0.115	0.025	0.025	0.015	0.028
LT/SN/Km2	1.91	3.32	2.39	5.17	10.0	7.25	8.14	2.02	0.440	0.432	0.261	0.495
AKIM mm.	5.13	8.61	6.41	13.9	24.2	19.4	21.1	5.40	1.14	1.16	0.700	1.28
MİL. M3	0.292	0.491	0.365	0.790	1.38	1.11	1.20	0.308	0.065	0.066	0.040	0.073

SU YILI (2006) YILLIK TOPLAM AKIM 6.18 MİLYON M3 108 MM. 3.4 LT/SN/Km2

16. Konya Kapali Havzasi

D16A172 Dari D. Oglakci

YERİ : **SEYDİŞEHIR OĞLAKCI KÖYÜ**
0°0'0" Doğu - 0°0'0" Kuzey

YAĞIŞ ALANI : **---- km2** **YAKLAŞIK KOT : 0 m**

GÖZLEM SÜRESİ : **01.10.2005 - 30.09.2006**

ORTALAMA AKIMLAR : **Gözlem süresinde 0.110 m3/sn. (1 Yıllık) 2006 Su yılında 0.110 m3/sn.**

ANLIK EN ÇOK VE EN AZ AKIMLAR:

2006 Su yılında anlık ençok akım	**:**	**8.90**	**m3/sn**	**18.08.2006**
2006 Su yılında anlık enaz akım	**:**	**0.007**	**m3/sn**	**19.06.2006**
Gözlem süresinde anlık ençok akım	**:**	**8.90**	**m3/sn**	**18.08.2006**
Gözlem süresinde anlık enaz akım	**:**	**0.007**	**m3/sn**	**19.06.2006**

İstasyon için kullanılmış anahtar bulunamadı.

Akımlar 01 Ekim 2005 'den 30 Eylül 2006' a kadar m3/sn olarak

Gün	Ekim	Kasım	Aralık	Ocak	Şubat	Mart	Nisan	Mayıs	Haziran	Temmuz	Ağustos	Eylül
01	0.047	0.071	0.071	0.095	0.095	0.240	0.512	0.139	0.035	0.035	0.019	0.044
02	0.047	0.071	0.071	0.095	0.095	0.264	0.436	0.150	0.035	0.024	0.019	0.039
03	0.047	0.071	0.071	0.095	0.083	0.474	0.360	0.150	0.030	0.024	0.019	0.034
04	0.047	0.117	0.071	0.083	0.047	0.474	0.336	0.168	0.030	0.019	0.019	0.029
05	0.047	0.117	0.071	0.083	0.035	0.398	0.288	0.168	0.024	0.019	0.024	0.024
06	0.047	0.106	0.071	0.083	0.047	0.336	0.222	0.150	0.024	0.019	0.024	0.019
07	0.047	0.106	0.071	0.083	0.059	0.288	0.204	0.150	0.024	0.019	0.024	0.019
08	0.035	0.106	0.071	0.083	0.047	0.288	0.186	0.139	0.019	0.019	0.024	0.016
09	0.030	0.106	0.071	0.071	0.071	0.264	0.168	0.128	0.019	0.019	0.024	0.016
10	0.035	0.106	0.071	0.106	0.083	0.204	0.186	0.128	0.019	0.019	0.024	0.019
11	0.035	0.106	0.071	0.128	0.095	0.186	0.186	0.117	0.013	0.019	0.024	0.024
12	0.059	0.095	0.071	0.139	0.106	0.186	0.168	0.106	0.013	0.019	0.019	0.024
13	0.059	0.095	0.071	0.106	0.117	0.288	0.150	0.106	0.013	0.019	0.019	0.024
14	0.059	0.095	0.071	0.071	0.128	0.288	0.150	0.106	0.013	0.019	0.019	0.024
15	0.059	0.095	0.071	0.071	0.139	0.288	0.168	0.106	0.013	0.019	0.019	0.024
16	0.106	0.095	0.071	0.071	0.139	0.312	0.204	0.106	0.013	0.019	0.024	0.019
17	0.071	0.095	0.071	0.071	0.139	0.336	0.150	0.106	0.013	0.019	0.024	0.019
18	0.071	0.095	0.083	0.083	0.106	0.360	0.139	0.106	0.013	0.019	0.090	0.024
19	0.071	0.095	0.095	0.071	0.035	0.398	0.139	0.106	0.013	0.019	0.090	0.029
20	0.071	0.095	0.106	0.083	0.047	0.512	0.128	0.095	0.013	0.019	0.072	0.024
21	0.071	0.095	0.117	0.071	0.059	0.786	0.128	0.071	0.013	0.019	0.072	0.024
22	0.071	0.095	0.117	0.071	0.071	0.786	0.128	0.035	0.013	0.019	0.072	0.029
23	0.071	0.083	0.117	0.071	0.095	0.878	0.128	0.035	0.013	0.019	0.072	0.029
24	0.083	0.083	0.106	0.059	0.106	0.878	0.312	0.035	0.013	0.019	0.072	0.029
25	0.071	0.083	0.139	0.071	0.139	0.786	0.168	0.035	0.013	0.019	0.072	0.034
26	0.071	0.083	0.240	0.083	0.204	0.702	0.128	0.071	0.013	0.019	0.062	0.034
27	0.071	0.071	0.240	0.071	0.204	0.702	0.128	0.095	0.013	0.019	0.062	0.029
28	0.071	0.071	0.186	0.083	0.186	0.702	0.128	0.083	0.013	0.019	0.062	0.029
29	0.071	0.071	0.106	0.095	-----	0.626	0.128	0.047	0.030	0.019	0.062	0.034
30	0.071	0.071	0.095	0.106	-----	0.588	0.139	0.035	0.035	0.019	0.053	0.039
31	0.071	-----	0.095	0.095	-----	0.664	-----	0.035	-----	0.019	0.053	-----
Maks.	0.222	0.222	0.336	0.240	0.288	1.11	0.664	0.186	0.095	0.059	8.90	0.053
Min.	0.030	0.059	0.047	0.059	0.035	0.150	0.128	0.035	0.007	0.013	0.019	0.016
Ortalama	0.061	0.091	0.098	0.085	0.099	0.467	0.200	0.100	0.019	0.020	0.043	0.027
LT/SN/Km2	0.000	0.000	0.000	0.000	0.000	0.000	0.000	0.000	0.000	0.000	0.000	0.000
AKIM mm.	0.000	0.000	0.000	0.000	0.000	0.000	0.000	0.000	0.000	0.000	0.000	0.000
MİL. M3	0.163	0.237	0.263	0.229	0.240	1.25	0.518	0.268	0.048	0.053	0.115	0.069

SU YILI (2006) YILLIK TOPLAM AKIM 3.45 MİLYON M3 0 MM. 0.0 LT/SN/Km2

17
DOĞU AKDENİZ HAVZASI

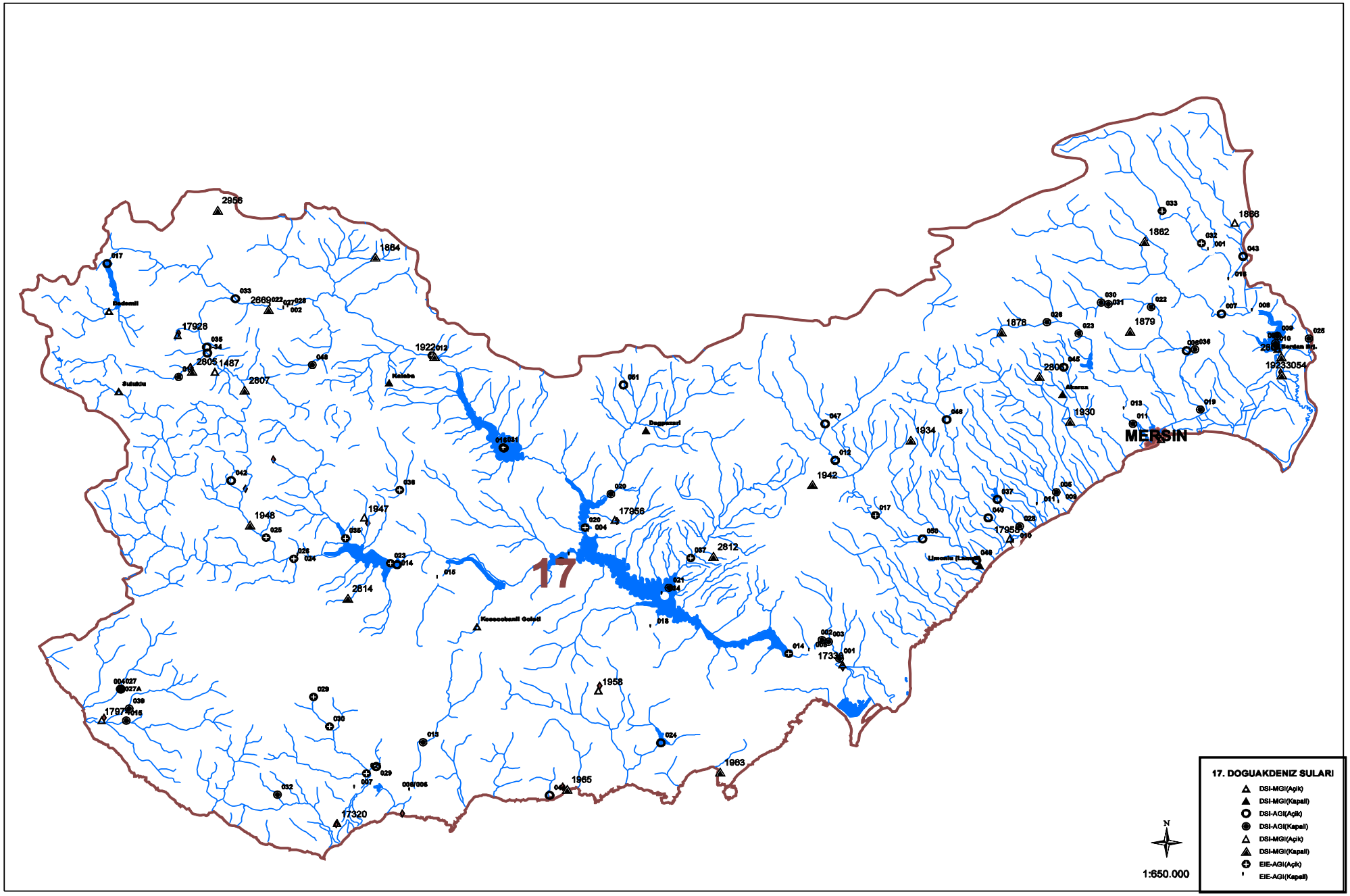
17
MERSIN
17. DOGUAKDENIZ SULARI
DSI-MGI(Açik)
DSI-MGI(Kapali)
DSI-AGI(Açik)
DSI-AGI(Kapali)
DSI-MGI(Açik)
DSI-MGI(Kapali)
EIE-AGI(Açik)
EIE-AGI(Kapali)
N
1:650.000

17. Dogu Akdeniz Havzasi

D17A006 DELİÇAY PUĞKARAAĞAÇ

YERİ : **MERSİN İLİ MERKEZ İLÇEYE BAĞLI PUĞKARAAĞAÇ KÖYÜNDEDİR.**
34°41'27" Doğu - 36°57'47" Kuzey

YAĞIŞ ALANI : **331,00 km2** **YAKLAŞIK KOT : 130 m**

GÖZLEM SÜRESİ : **01.04.1995 - 30.09.2006**

ORTALAMA AKIMLAR : **Gözlem süresinde 1.178 m3/sn. (7 Yıllık) 2006 Su yılında 0.446 m3/sn.**

ANLIK EN ÇOK VE EN AZ AKIMLAR:

2006 Su yılında anlık ençok akım	:	**34.7**	**m3/sn**	**04.11.2005**
2006 Su yılında anlık enaz akım	:	**0.027**	**m3/sn**	**03.06.2006**
Gözlem süresinde anlık ençok akım	:	**330.**	**m3/sn**	**25.12.1966**
Gözlem süresinde anlık enaz akım	:	**0.000**	**m3/sn**	**01.10.1966**

6. Anahtar Eğrisi (Seviyeler cm olarak)

Seviye	Akım	Seviye	Akım	Seviye	Akım	Seviye	Akım
24	0.027	44	1.8	140	43.3	290	141.
27	0.081	49	2.7	170	61.2	320	162.
30	0.195	59	5.0	200	80.1	350	183.
33	0.366	80	12.1	230	99.4	380	204.
38	0.834	110	26.3	260	120.		

Akımlar 01 Ekim 2005 'den 30 Eylül 2006' a kadar m3/sn olarak

Gün	Ekim	Kasım	Aralık	Ocak	Şubat	Mart	Nisan	Mayıs	Haziran	Temmuz	Ağustos	Eylül
01	0.113	0.195	0.433	0.433	0.433	0.433	0.730	0.284	0.059	0.081	0.113	0.081
02	0.059	0.195	0.366	0.433	0.433	0.433	0.834	0.284	0.059	0.081	0.059	0.081
03	0.059	0.195	0.366	0.433	0.433	0.433	0.730	0.284	0.039	0.147	0.059	0.081
04	0.059	6.84	0.366	0.366	0.366	0.366	0.730	0.366	0.039	0.366	0.059	0.059
05	0.059	0.834	0.366	0.366	0.366	0.366	0.730	0.284	0.039	0.530	0.059	0.059
06	0.059	0.626	0.366	0.366	0.284	0.366	0.626	0.239	0.059	0.530	0.059	0.059
07	0.059	0.530	0.366	0.366	3.57	0.284	0.626	0.239	0.039	0.962	0.081	0.059
08	0.059	0.530	0.366	0.433	7.45	0.366	0.626	0.239	0.039	0.366	0.081	0.059
09	0.059	0.433	0.284	0.433	4.01	2.31	0.626	0.239	0.059	0.195	0.081	0.059
10	0.059	0.433	0.284	0.433	1.94	1.25	0.626	0.195	0.039	0.147	0.059	0.059
11	0.059	0.433	0.239	0.433	3.34	0.834	0.530	0.195	0.059	0.147	0.059	0.059
12	0.059	0.433	0.239	0.433	2.48	0.730	0.530	0.195	0.113	0.147	0.081	0.027
13	0.059	0.433	0.195	0.366	1.94	0.730	0.626	0.195	0.284	0.113	0.113	0.113
14	0.059	0.433	0.147	0.366	1.58	5.92	0.626	0.147	0.195	0.113	0.147	0.147
15	0.059	0.433	0.239	0.284	1.40	3.57	0.530	0.147	0.147	0.113	0.081	0.195
16	0.530	0.433	0.284	0.284	1.09	2.48	0.530	0.147	0.113	0.113	0.081	0.081
17	0.433	0.433	0.284	0.284	0.962	2.13	0.530	0.284	0.081	0.113	0.081	0.081
18	0.366	0.433	0.284	0.284	0.834	1.76	0.530	0.284	0.059	0.113	0.081	0.113
19	0.366	0.433	0.834	0.284	0.834	1.58	0.530	0.239	0.081	0.081	0.059	0.081
20	0.366	0.433	0.530	0.239	0.730	1.40	0.433	0.195	0.059	0.059	0.059	0.039
21	0.530	0.433	0.366	0.239	0.730	1.25	0.433	0.195	0.059	0.059	0.059	0.039
22	0.433	0.433	0.284	0.239	0.626	1.09	0.433	0.195	0.039	0.027	0.039	0.039
23	0.433	0.433	0.284	0.284	0.530	1.09	0.433	0.147	0.039	0.039	0.059	0.081
24	0.433	0.433	0.239	0.284	0.530	0.962	0.433	0.147	0.059	0.039	0.059	0.113
25	0.433	0.433	0.239	1.40	0.530	0.962	0.433	0.147	0.059	0.039	0.059	0.113
26	0.366	0.433	0.284	1.25	0.530	0.962	0.366	0.113	0.059	0.059	0.059	0.081
27	0.239	0.433	0.626	0.834	0.433	0.962	0.366	0.081	0.081	0.081	0.039	0.081
28	0.239	0.433	0.530	0.626	0.433	0.834	0.366	0.081	0.081	0.113	0.027	0.081
29	0.239	0.433	0.433	0.530	-----	0.834	0.366	0.081	0.195	0.113	0.039	0.081
30	0.239	0.433	0.433	0.530	-----	0.834	0.366	0.059	0.147	0.113	0.081	0.059
31	0.195	-----	0.433	0.433	-----	0.730	-----	0.059	-----	0.113	0.081	-----
Maks.	6.53	34.7	5.62	5.31	31.3	19.2	0.962	1.09	0.626	3.34	0.147	0.366
Min.	0.059	0.195	0.113	0.195	0.284	0.284	0.366	0.039	0.027	0.027	0.027	0.027
Ortalama	0.219	0.649	0.354	0.451	1.39	1.23	0.542	0.193	0.083	0.171	0.069	0.079
LT/SN/Km2	0.661	1.96	1.07	1.36	4.19	3.73	1.64	0.583	0.250	0.518	0.210	0.238
AKIM mm.	1.77	5.08	2.87	3.65	10.1	9.98	4.25	1.56	0.647	1.39	0.562	0.616
MİL. M3	0.586	1.68	0.949	1.21	3.35	3.30	1.41	0.517	0.214	0.459	0.186	0.204

SU YILI (2006) YILLIK TOPLAM AKIM 14.06 MİLYON M3 42 MM. 1.3 LT/SN/Km2

17. Dogu Akdeniz Havzasi

D17A007 PAMUK DERE KEŞBÜKÜ

YERİ : TARSUS-NAMRUN YOLUNUN 23 KM.SİNDEKİ KEŞKÜLLÜ MEVKİİNDEKİ KEŞBÜKÜ KÖPRÜSÜNÜN 300 M. MANSABINDADIR.
34°46'6" Doğu - 37°1'50" Kuzey

YAĞIŞ ALANI : 599,00 km2 **YAKLAŞIK KOT** : 132 m

GÖZLEM SÜRESİ : 19.10.1959 - 30.09.2006

ORTALAMA AKIMLAR : Gözlem süresinde 12.318 m3/sn. (43 Yıllık) 2006 Su yılında 7.801 m3/sn.

ANLIK EN ÇOK VE EN AZ AKIMLAR:

2006 Su yılında anlık ençok akım	:	51.6	m3/sn	17.04.2006
2006 Su yılında anlık enaz akım	:	0.844	m3/sn	26.11.2005
Gözlem süresinde anlık ençok akım	:	396.	m3/sn	08.12.2001
Gözlem süresinde anlık enaz akım	:	0.695	m3/sn	06.11.2004

22. Anahtar Eğrisi (Seviyeler cm olarak)

Seviye	Akım	Seviye	Akım	Seviye	Akım	Seviye	Akım
8	0.695	50	11.1	320	145.	430	250.
11	1.2	80	22.6	350	175.	440	260.
14	1.7	110	35.4	380	200.	450	270.
17	2.3	140	49.2	410	230.	460	280.
20	2.9	170	63.6	420	240.	600	420.

Akımlar 01 Ekim 2005 'den 30 Eylül 2006' a kadar m3/sn olarak

Gün	Ekim	Kasım	Aralık	Ocak	Şubat	Mart	Nisan	Mayıs	Haziran	Temmuz	Ağustos	Eylül
01	3.58	2.70	4.96	3.35	2.48	6.53	17.0	19.7	15.8	6.26	4.04	1.89
02	1.53	3.58	4.04	1.53	2.48	7.07	21.0	19.7	15.5	6.26	3.81	1.89
03	1.89	3.12	3.12	3.58	2.70	7.60	19.7	20.1	15.5	6.80	2.89	1.89
04	2.89	4.27	6.26	2.26	2.48	8.19	19.3	18.1	15.1	6.26	2.48	1.89
05	3.12	8.52	3.81	2.89	2.70	8.19	17.4	16.6	14.3	6.53	2.70	1.89
06	1.71	4.27	4.50	2.48	2.89	7.60	16.2	16.6	15.1	7.33	2.70	1.71
07	2.48	4.73	3.81	2.70	6.80	7.60	17.0	17.4	14.0	7.87	2.48	1.71
08	1.37	4.04	4.27	2.48	13.6	7.87	21.4	17.7	12.2	8.52	2.70	1.89
09	2.48	3.81	3.58	2.26	11.8	10.8	21.4	18.1	10.5	6.53	2.48	1.71
10	4.04	3.58	3.58	2.48	9.16	9.16	28.9	16.6	9.49	5.73	2.48	1.71
11	1.71	3.35	2.70	3.81	7.60	8.19	30.2	16.6	8.52	5.46	2.48	1.71
12	2.08	3.35	3.12	2.26	8.19	7.60	30.2	18.5	6.80	4.96	2.48	1.71
13	3.12	3.12	3.12	1.71	7.33	7.60	34.5	20.6	7.33	4.73	2.48	1.71
14	2.26	2.70	2.70	1.89	6.53	12.2	35.0	18.9	8.84	4.73	2.48	1.71
15	1.53	2.70	3.35	2.26	5.99	19.3	30.6	17.7	7.33	4.50	2.26	1.71
16	1.53	2.70	3.35	2.89	5.19	14.7	38.2	18.5	8.84	4.50	2.26	1.71
17	3.12	2.26	3.35	2.26	4.73	12.2	42.3	17.0	8.19	4.27	2.48	1.71
18	4.96	2.89	3.35	2.26	4.50	12.5	36.3	15.8	7.07	4.73	2.08	1.53
19	5.99	5.19	7.60	2.26	4.50	12.2	29.7	15.5	7.07	4.50	2.08	1.53
20	5.73	6.26	6.80	2.26	4.96	11.5	31.4	15.8	7.07	4.27	2.08	1.53
21	5.73	9.81	5.73	2.26	4.73	10.1	30.2	16.6	7.07	4.27	1.89	1.89
22	2.48	5.73	4.73	2.26	5.73	11.1	28.5	17.7	7.33	4.27	2.08	1.53
23	2.89	3.81	4.27	2.26	6.80	14.7	26.8	20.6	6.53	4.27	1.71	1.71
24	2.48	3.35	4.73	2.70	7.33	18.1	25.1	22.2	7.07	4.04	1.89	1.53
25	3.12	3.35	4.04	3.58	7.60	17.7	22.2	20.6	6.53	4.04	2.08	1.53
26	3.35	3.81	3.58	4.27	8.19	17.0	19.3	19.3	6.53	4.04	2.08	1.71
27	3.35	3.58	2.70	4.27	8.19	14.7	18.1	19.7	6.80	3.81	2.08	1.71
28	2.48	5.99	3.58	3.58	6.80	14.3	17.7	18.9	5.46	3.81	1.89	1.53
29	2.89	4.96	2.89	2.70	-----	14.7	17.4	18.1	6.26	4.27	1.89	1.53
30	2.48	4.50	3.12	2.70	-----	15.1	17.7	17.0	6.26	4.04	1.89	1.71
31	2.26	-----	2.89	2.48	-----	17.7	-----	17.0	-----	4.04	2.08	-----
Maks.	6.53	18.1	15.1	11.1	20.6	22.2	51.6	29.3	19.7	20.1	10.8	8.84
Min.	0.999	0.844	0.999	0.999	1.20	2.70	11.1	15.1	4.73	1.89	0.999	0.844
Ortalama	2.92	4.20	3.99	2.68	6.14	11.7	25.4	18.2	9.35	5.15	2.37	1.70
LT/SN/Km2	4.88	7.01	6.66	4.47	10.3	19.6	42.3	30.3	15.6	8.60	3.96	2.84
AKIM mm.	13.1	18.2	17.8	12.0	24.8	52.5	110.	81.2	40.4	23.0	10.6	7.37
MİL. M3	7.83	10.9	10.7	7.17	14.9	31.4	65.7	48.7	24.2	13.8	6.35	4.42

SU YILI (2006) YILLIK TOPLAM AKIM 246.07 MİLYON M3 411 MM. 13.0 LT/SN/Km2

17. Dogu Akdeniz Havzasi

D17A011 EFRENK DERESİ HAMZABEYLİ

YERİ : **MERSİN İLİ KARAİSALI-IŞIKLITEPE KÖYÜ YOLUNUN 12 KM SİNDEKI HAMZABEYLİ KÖYÜ KÖPRÜSÜNDEDİR**
34°33'11" Doğu - 36°51'42" Kuzey

YAĞIŞ ALANI : **410,00 km2** **YAKLAŞIK KOT : 125 m**

GÖZLEM SÜRESİ : **17.12.1964 - 30.09.2006**

ORTALAMA AKIMLAR : **Gözlem süresinde 2.547 m3/sn. (37 Yıllık) 2006 Su yılında 0.672 m3/sn.**

ANLIK EN ÇOK VE EN AZ AKIMLAR:

2006 Su yılında anlık ençok akım	:	**7.58**	**m3/sn**	**07.02.2006**
2006 Su yılında anlık enaz akım	:	**0.007**	**m3/sn**	**18.09.2006**
Gözlem süresinde anlık ençok akım	:	**150.**	**m3/sn**	**05.05.2000**
Gözlem süresinde anlık enaz akım	:	**0.002**	**m3/sn**	**20.09.1985**

Akımlar 01 Ekim 2005 'den 30 Eylül 2006' a kadar m3/sn olarak

Gün	Ekim	Kasım	Aralık	Ocak	Şubat	Mart	Nisan	Mayıs	Haziran	Temmuz	Ağustos	Eylül
01	0.024	0.455	0.455	0.455	0.455	1.02	2.51	0.841	0.455	0.188	0.131	0.065
02	0.024	0.516	0.316	0.455	0.455	1.02	2.68	0.907	0.516	0.269	0.131	0.065
03	0.024	0.516	0.316	0.455	0.455	1.14	2.51	0.907	0.269	0.269	0.131	0.065
04	0.029	1.48	0.316	0.386	0.455	1.14	2.51	0.841	0.316	0.386	0.131	0.038
05	0.029	0.708	0.316	0.386	0.455	1.25	2.34	0.841	0.386	0.386	0.131	0.038
06	0.029	0.516	0.316	0.386	0.455	1.14	1.99	0.841	0.386	0.386	0.131	0.047
07	0.029	0.516	0.222	0.386	1.37	1.14	1.99	0.775	0.455	0.576	0.109	0.038
08	0.038	0.455	0.222	0.386	4.33	1.25	2.34	0.841	0.269	0.455	0.109	0.029
09	0.038	0.455	0.316	0.386	3.42	2.51	2.16	0.841	0.269	0.455	0.109	0.038
10	0.038	0.386	0.316	0.386	2.34	1.82	2.51	0.775	0.269	0.386	0.087	0.038
11	0.038	0.386	0.386	0.386	2.68	1.65	2.34	0.775	0.269	0.386	0.065	0.029
12	0.038	0.455	0.316	0.386	2.34	1.65	2.34	0.775	0.386	0.269	0.065	0.029
13	0.047	0.455	0.316	0.386	1.99	1.65	2.68	0.708	0.386	0.222	0.065	0.029
14	0.047	0.455	0.316	0.316	1.65	3.02	2.34	0.642	0.386	0.222	0.065	0.024
15	0.065	0.455	0.386	0.316	1.48	4.10	1.99	0.642	0.386	0.188	0.065	0.024
16	0.222	0.455	0.386	0.269	1.37	3.42	2.51	0.775	0.455	0.188	0.065	0.029
17	0.455	0.455	0.386	0.269	1.25	3.02	2.16	0.775	0.109	0.188	0.065	0.024
18	0.386	0.455	0.316	0.316	1.14	2.68	1.65	0.642	0.109	0.153	0.065	0.013
19	0.455	0.516	0.455	0.316	1.14	2.51	1.37	0.576	0.153	0.153	0.065	0.013
20	0.576	0.516	0.642	0.455	1.02	2.34	1.25	0.576	0.087	0.087	0.065	0.019
21	0.455	0.516	0.576	0.386	0.907	2.16	1.14	0.576	0.087	0.065	0.065	0.024
22	0.455	0.455	0.576	0.269	0.907	2.16	1.14	0.516	0.065	0.065	0.065	0.047
23	0.455	0.455	0.516	0.222	0.907	2.34	1.02	0.516	0.131	0.065	0.065	0.222
24	0.455	0.455	0.516	0.222	0.907	2.68	1.02	0.316	0.087	0.065	0.065	0.269
25	0.316	0.455	0.516	0.708	0.907	2.68	1.02	0.316	0.087	0.109	0.065	0.188
26	0.316	0.455	0.455	0.841	0.907	2.68	0.907	0.455	0.109	0.109	0.065	0.153
27	0.316	0.455	0.516	0.642	1.02	2.51	0.907	0.455	0.109	0.109	0.065	0.153
28	0.269	0.455	0.455	0.576	1.02	2.51	0.907	0.516	0.109	0.109	0.065	0.131
29	0.316	0.455	0.455	0.516	-----	2.34	0.907	0.576	0.153	0.109	0.065	0.131
30	0.386	0.455	0.455	0.516	-----	2.34	0.841	0.576	0.269	0.131	0.065	0.109
31	0.455	-----	0.455	0.516	-----	2.51	-----	0.455	-----	0.131	0.065	-----
Maks.	0.841	1.48	0.708	1.48	7.58	6.79	3.19	1.02	0.576	0.841	0.131	1.48
Min.	0.013	0.386	0.222	0.222	0.455	1.02	0.841	0.269	0.065	0.065	0.065	0.007
Ortalama	0.220	0.507	0.403	0.416	1.35	2.14	1.80	0.664	0.251	0.222	0.083	0.071
LT/SN/Km2	0.537	1.24	0.984	1.01	3.29	5.22	4.39	1.62	0.612	0.541	0.202	0.172
AKIM mm.	1.44	3.21	2.64	2.72	7.95	14.0	11.4	4.33	1.59	1.45	0.541	0.447
MİL. M3	0.590	1.31	1.08	1.11	3.26	5.74	4.66	1.78	0.650	0.594	0.222	0.183

SU YILI (2006) YILLIK TOPLAM AKIM 21.18 MİLYON M3 52 MM. 1.6 LT/SN/Km2

17. Dogu Akdeniz Havzasi

D17A012 LAMAS Ç. SARIAYDIN

YERİ : **MERSİN İLİ SİLİFKE İLÇESİ KIROBASI BUCAĞINA BAĞLI SARIAYDIN KÖYÜNDEDİR.**
33°54'58" Doğu - 36°45'43" Kuzey

YAĞIŞ ALANI : **156,40 km2** **YAKLAŞIK KOT : 1297 m**

GÖZLEM SÜRESİ : **01.10.1991 - 30.09.2006**

ORTALAMA AKIMLAR : **Gözlem süresinde 2.893 m3/sn. (14 Yıllık) 2006 Su yılında 1.762 m3/sn.**

ANLIK EN ÇOK VE EN AZ AKIMLAR:

2006 Su yılında anlık ençok akım	:	**12.3**	**m3/sn**	**27.03.2006**
2006 Su yılında anlık enaz akım	:	**0.700**	**m3/sn**	**03.09.2006**
Gözlem süresinde anlık ençok akım	:	**70.6**	**m3/sn**	**05.03.2004**
Gözlem süresinde anlık enaz akım	:	**0.380**	**m3/sn**	**03.01.1992**

3. Anahtar Eğrisi (Seviyeler cm olarak)

Seviye	Akım	Seviye	Akım	Seviye	Akım	Seviye	Akım
40	0.550	70	4.0	140	24.0	240	70.0
45	0.918	80	5.8	160	32.0	250	76.0
50	1.3	90	8.2	180	40.0	260	82.0
59	2.3	110	13.5	200	50.0	270	88.0
65	3.2	130	20.5	220	60.0	280	95.0

Akımlar 01 Ekim 2005 'den 30 Eylül 2006' a kadar m3/sn olarak

Gün	Ekim	Kasım	Aralık	Ocak	Şubat	Mart	Nisan	Mayıs	Haziran	Temmuz	Ağustos	Eylül
01	0.980	1.05	1.05	1.05	0.980	1.80	7.00	2.40	1.40	1.15	0.900	0.780
02	0.980	1.05	1.05	1.05	1.05	1.90	7.20	2.30	1.40	1.15	0.900	0.780
03	0.980	0.980	1.05	1.05	1.15	1.90	7.40	2.20	1.40	1.15	0.980	0.700
04	0.980	1.25	1.05	1.05	1.15	3.70	7.60	2.20	1.40	1.15	0.840	0.780
05	0.980	1.05	1.05	1.05	1.05	3.10	7.00	2.10	1.40	1.15	0.780	0.780
06	0.980	1.05	1.05	0.980	1.05	2.40	8.30	2.10	1.50	1.15	0.780	0.700
07	0.980	1.05	1.05	0.980	1.40	2.20	7.20	2.10	1.40	1.05	0.780	0.780
08	0.980	1.05	1.05	0.980	1.25	2.00	6.60	2.10	1.40	1.05	0.840	0.700
09	0.980	0.980	1.05	0.980	1.15	2.00	6.40	2.00	1.40	1.05	0.900	0.700
10	0.980	0.980	1.05	0.980	1.05	2.85	6.00	2.00	1.40	1.05	0.840	0.700
11	0.980	0.980	1.05	0.980	0.980	2.10	6.00	2.00	1.40	1.05	0.840	0.780
12	0.980	0.980	1.05	0.980	0.980	2.85	7.40	2.00	1.40	0.980	0.900	0.980
13	0.980	0.980	1.05	0.980	1.05	2.55	7.00	1.90	1.35	0.980	0.840	0.900
14	0.980	0.980	1.05	0.980	0.980	2.55	5.40	1.90	1.35	0.980	0.840	0.840
15	0.980	0.980	1.05	0.980	1.05	2.70	4.60	1.90	1.35	0.900	0.780	0.840
16	0.980	0.980	1.05	0.980	1.05	2.70	4.20	1.80	1.35	1.05	0.780	0.840
17	0.980	0.980	1.05	0.900	1.05	3.00	4.00	1.50	1.40	0.900	0.780	0.840
18	0.980	0.980	1.05	0.980	1.05	3.60	3.70	1.80	1.50	0.980	0.780	0.840
19	0.980	1.15	1.15	0.980	1.15	5.80	3.60	1.80	1.40	0.900	0.780	0.780
20	0.980	1.15	1.15	0.980	1.05	7.80	3.50	1.80	1.35	0.980	0.840	0.780
21	0.980	1.15	1.15	1.15	1.25	8.30	3.35	1.80	1.25	0.980	0.840	0.840
22	0.980	1.15	1.05	1.15	1.35	7.40	3.10	1.70	1.25	0.980	0.780	0.840
23	0.980	1.15	1.05	1.15	1.35	7.20	3.00	1.60	1.40	0.980	0.780	0.840
24	0.980	1.15	1.05	1.05	1.35	8.00	2.85	1.60	1.40	0.980	0.780	0.840
25	0.980	1.15	0.980	1.05	1.35	8.00	2.70	1.50	1.40	0.900	0.840	0.840
26	0.980	1.15	1.05	1.05	1.35	8.60	3.00	1.60	1.40	0.900	0.840	0.840
27	0.980	1.15	1.05	1.05	1.40	10.5	2.85	1.60	1.25	0.900	0.780	0.840
28	0.980	1.05	1.05	1.05	1.50	9.40	2.55	1.60	1.25	0.900	0.780	0.840
29	0.980	1.05	1.05	1.15	-----	11.0	2.55	1.70	1.25	0.900	0.780	0.840
30	0.980	1.05	1.05	0.900	-----	9.40	2.55	1.60	1.15	0.900	0.780	0.840
31	1.05	-----	1.05	0.980	-----	8.60	-----	1.60	-----	0.900	0.780	-----
Maks.	1.05	1.40	1.25	1.35	1.60	12.3	9.80	2.55	1.60	1.25	0.980	1.05
Min.	0.980	0.980	0.900	0.780	0.900	1.60	2.30	1.50	1.15	0.840	0.780	0.700
Ortalama	0.982	1.06	1.06	1.02	1.16	5.03	4.95	1.86	1.37	1.00	0.821	0.807
LT/SN/Km2	6.28	6.78	6.76	6.52	7.44	32.2	31.7	11.9	8.73	6.40	5.25	5.16
AKIM mm.	16.8	17.6	18.1	17.5	18.0	86.1	82.1	31.9	22.6	17.1	14.1	13.4
MİL. M3	2.63	2.75	2.83	2.73	2.81	13.5	12.8	4.99	3.54	2.68	2.20	2.09

SU YILI (2006) YILLIK TOPLAM AKIM 55.55 MİLYON M3 355 MM. 11.3 LT/SN/Km2

17. Dogu Akdeniz Havzasi

D17A014 Göksu N. Görmel Köp.

YERİ : **İstasyona Ait Adres Bilgisi Girilmemiştir.**
32°57'23" Doğu - 36°33'46" Kuzey

YAĞIŞ ALANI : **2156,00 km2** **YAKLAŞIK KOT : 509 m**

GÖZLEM SÜRESİ : **01.11.1963 - 30.09.2006**

ORTALAMA AKIMLAR : **Gözlem süresinde 45.323 m3/sn. (37 Yıllık) 2006 Su yılında 29.441 m3/sn.**

ANLIK EN ÇOK VE EN AZ AKIMLAR:

2006 Su yılında anlık ençok akım	**:**	**197.**	**m3/sn**	**17.04.2006**
2006 Su yılında anlık enaz akım	**:**	**4.76**	**m3/sn**	**20.09.2006**
Gözlem süresinde anlık ençok akım	**:**	**1748**	**m3/sn**	**25.11.2001**
Gözlem süresinde anlık enaz akım	**:**	**4.10**	**m3/sn**	**10.09.1983**

İstasyon için kullanılmış anahtar bulunamadı.

Akımlar 01 Ekim 2005 'den 30 Eylül 2006' a kadar m3/sn olarak

Gün	Ekim	Kasım	Aralık	Ocak	Şubat	Mart	Nisan	Mayıs	Haziran	Temmuz	Ağustos	Eylül
01	7.59	8.77	19.5	15.4	20.1	49.6	125.	56.5	22.7	11.2	6.76	5.14
02	7.59	8.62	18.8	15.1	19.8	45.8	106.	52.7	21.4	11.0	6.76	5.14
03	7.59	9.22	16.6	15.1	19.5	49.6	129.	50.2	20.8	10.8	7.00	5.52
04	7.59	9.22	16.0	15.1	20.1	55.3	126.	49.6	20.4	10.8	7.00	5.52
05	7.59	15.9	16.6	15.7	21.7	63.5	116.	46.4	19.5	11.2	7.00	5.52
06	7.00	14.3	17.2	15.7	22.4	62.2	97.1	42.0	18.8	12.7	7.00	5.14
07	7.00	11.8	16.6	16.3	22.7	53.4	97.8	40.7	18.2	10.7	6.76	5.14
08	7.00	11.4	15.4	16.9	46.4	59.0	109.	36.7	17.5	10.7	6.76	5.14
09	7.00	10.9	14.5	17.5	57.2	66.0	119.	37.9	16.3	9.46	6.76	5.14
10	7.00	10.7	13.9	17.2	39.3	66.6	114.	36.7	16.0	8.92	6.76	5.14
11	7.00	10.4	13.6	16.6	37.9	50.8	120.	34.7	15.4	8.77	6.76	5.14
12	7.59	10.4	13.0	16.0	136.	45.1	115.	34.3	14.8	8.47	6.76	5.14
13	7.59	10.2	12.7	15.7	101.	42.6	123.	35.1	14.5	8.18	6.52	5.14
14	7.59	10.2	12.7	15.4	76.6	50.2	129.	35.1	14.2	8.18	6.52	5.14
15	7.59	10.2	12.4	14.8	45.8	63.5	140.	35.9	13.9	7.88	6.52	5.14
16	8.18	10.2	12.4	14.5	36.7	62.2	134.	34.7	13.9	7.88	6.28	5.14
17	9.46	10.2	13.0	14.2	31.5	60.3	197.	32.7	13.6	8.18	6.28	5.14
18	9.22	10.2	14.5	13.9	28.8	52.7	175.	30.4	13.3	7.88	6.28	5.14
19	9.22	10.7	41.3	13.9	27.2	50.2	131.	29.2	12.7	7.88	6.28	5.14
20	9.22	27.6	75.9	13.9	28.4	70.4	103.	31.2	12.4	7.59	6.28	4.76
21	9.22	44.5	80.4	57.2	30.4	62.8	108.	30.8	12.4	7.59	6.28	4.76
22	9.22	81.2	33.5	31.2	30.4	58.4	104.	32.3	12.1	7.29	6.28	5.14
23	9.22	36.3	26.0	22.7	33.1	65.4	86.5	32.7	11.8	7.29	5.90	5.14
24	9.22	25.6	23.0	23.7	35.1	78.9	79.7	34.3	11.5	7.29	5.90	5.52
25	9.22	20.1	20.8	24.8	36.7	110.	72.3	33.5	11.5	7.00	6.28	5.90
26	9.22	18.2	19.1	43.2	38.3	112.	61.6	33.1	11.5	7.00	5.90	6.52
27	9.07	16.9	17.8	36.3	45.8	97.1	50.2	29.6	11.5	7.00	5.52	7.59
28	8.92	16.0	16.9	28.0	50.8	97.1	45.8	28.0	11.8	6.76	5.52	7.00
29	8.92	15.7	16.3	23.7	-----	100.	48.3	26.8	11.8	6.76	5.52	6.52
30	8.92	16.3	16.0	21.7	-----	108.	48.3	24.8	11.5	6.76	5.52	6.52
31	8.92	-----	16.0	20.8	-----	108.	-----	23.7	-----	6.76	5.14	-----
Maks.	9.70	81.2	80.4	57.2	136.	112.	197.	56.5	22.7	12.7	7.00	7.59
Min.	7.00	8.62	12.4	13.9	19.5	42.6	45.8	23.0	11.5	6.76	5.14	4.76
Ortalama	8.25	17.4	21.7	20.7	40.7	68.3	107.	35.9	14.9	8.58	6.35	5.47
LT/SN/Km2	3.83	8.07	10.1	9.61	18.9	31.7	49.6	16.6	6.92	3.98	2.94	2.54
AKIM mm.	10.2	20.9	26.9	25.7	45.7	84.8	129.	44.6	17.9	10.7	7.89	6.58
MİL. M3	22.1	45.1	58.1	55.5	98.5	183.	277.	96.1	38.7	23.0	17.0	14.2

SU YILI (2006) YILLIK TOPLAM AKIM 928.30 MİLYON M3 431 MM. 13.7 LT/SN/Km2

17. Dogu Akdeniz Havzasi

D17A016 GÖKSU N. KRAVGA KÖPRÜSÜ

YERİ : **MUT-ERMENEK YOLUNUN 30.KM.SİNDE SAĞA AYRILAN KÖPRÜBAŞI KÖYÜ YOLUNUN 7.KM.SİNDEKİ KRAVGA (GÖKSU) BELDESİNDEKI KÖPRÜDEDİR.**
33°11'15" Doğu - 36°46'54" Kuzey

YAĞIŞ ALANI : **2994,00 km2** **YAKLAŞIK KOT : 233 m**

GÖZLEM SÜRESİ : **01.07.1964 - 30.09.2006**

ORTALAMA AKIMLAR : **Gözlem süresinde 35.652 m3/sn. (37 Yıllık) 2006 Su yılında 23.615 m3/sn.**

ANLIK EN ÇOK VE EN AZ AKIMLAR:

2006 Su yılında anlık ençok akım	**:**	**135.**	**m3/sn**	**16.04.2006**
2006 Su yılında anlık enaz akım	**:**	**8.60**	**m3/sn**	**26.06.2006**
Gözlem süresinde anlık ençok akım	**:**	**591.**	**m3/sn**	**28.12.2001**
Gözlem süresinde anlık enaz akım	**:**	**0.010**	**m3/sn**	**07.09.2000**

30. Anahtar Eğrisi (Seviyeler cm olarak)

Seviye	Akım	Seviye	Akım	Seviye	Akım	Seviye	Akım
25	1.9	90	28.7	200	166.	330	423.
30	2.6	110	44.0	230	224.	340	443.
40	4.4	125	57.5	260	285.	350	463.
55	8.6	140	75.1	290	345.	380	538.
74	18.0	170	117.	320	404.	406	603.

Akımlar 01 Ekim 2005 'den 30 Eylül 2006' a kadar m3/sn olarak

Gün	Ekim	Kasım	Aralık	Ocak	Şubat	Mart	Nisan	Mayıs	Haziran	Temmuz	Ağustos	Eylül
01	11.7	11.7	13.1	13.6	16.1	44.0	75.1	35.3	16.8	15.0	12.1	11.2
02	11.7	11.7	13.1	14.1	16.1	45.8	81.8	34.5	16.8	15.0	12.1	11.7
03	11.7	11.7	14.1	13.1	16.1	49.4	80.4	36.0	16.1	15.0	12.1	11.7
04	11.2	14.1	13.6	13.1	16.1	53.9	75.1	35.3	16.1	14.1	12.1	11.7
05	11.2	14.1	13.1	13.6	18.6	56.6	65.2	34.5	15.5	15.0	12.1	11.7
06	11.2	13.6	13.6	13.6	19.2	52.1	60.8	33.1	15.5	14.5	12.1	11.2
07	11.2	13.1	13.6	13.6	27.2	52.1	61.9	30.9	15.5	14.5	12.1	11.2
08	11.2	13.1	13.1	13.6	44.9	55.7	67.4	29.4	15.5	14.5	12.1	11.2
09	11.2	13.1	13.1	14.1	36.8	54.8	67.4	28.7	15.5	14.5	11.7	11.7
10	11.2	12.6	12.6	14.1	31.6	45.8	66.3	27.2	15.0	14.5	11.7	11.7
11	11.2	12.6	12.6	14.1	30.9	40.8	60.8	26.5	15.5	14.5	11.7	11.2
12	11.2	12.1	12.6	14.5	37.6	38.4	60.8	25.7	15.5	14.5	11.7	11.2
13	11.2	12.1	12.1	15.0	42.4	46.7	61.9	25.0	15.5	14.1	11.7	11.2
14	11.2	12.1	12.6	14.5	38.4	53.0	68.5	24.2	15.5	14.1	11.7	11.2
15	11.2	12.1	12.6	14.5	33.1	54.8	72.5	24.2	15.5	14.1	11.7	11.2
16	11.2	12.1	12.6	14.1	32.4	52.1	93.8	23.6	15.5	13.6	11.7	11.7
17	11.2	11.7	12.6	14.1	30.9	48.5	120.	23.0	15.5	14.5	11.7	11.7
18	11.2	11.7	12.6	14.1	26.5	47.6	84.4	22.3	15.5	14.5	11.7	11.2
19	11.2	12.6	12.6	14.1	25.0	47.6	63.0	21.7	15.0	19.9	11.7	11.2
20	11.2	16.8	13.6	15.5	25.0	50.3	57.5	21.7	15.0	15.0	11.7	11.7
21	11.2	24.2	17.4	23.0	28.0	56.6	56.6	21.1	15.0	13.6	11.7	11.7
22	11.2	25.0	16.1	20.5	29.4	55.7	51.2	21.1	15.0	13.6	11.7	11.7
23	11.2	19.9	15.0	18.6	30.9	84.4	47.6	19.9	15.0	13.6	11.7	11.7
24	11.7	17.4	14.5	17.4	35.3	87.1	47.6	19.9	15.0	13.1	11.7	12.1
25	11.7	15.5	14.1	21.1	40.0	77.8	45.8	19.2	15.0	12.6	11.7	12.1
26	11.7	14.5	13.6	20.5	44.0	85.7	40.0	18.6	13.1	12.6	11.7	11.2
27	11.7	14.1	13.1	19.2	49.4	77.8	36.0	18.6	13.1	12.6	11.7	11.2
28	11.7	14.1	13.1	18.0	47.6	75.1	35.3	18.6	14.5	12.6	11.7	11.7
29	11.7	14.1	13.1	16.8	-----	73.8	35.3	18.0	15.0	12.6	11.7	11.2
30	11.7	13.6	13.1	16.1	-----	72.5	36.0	17.4	14.5	12.6	11.7	11.2
31	11.7	-----	13.1	16.1	-----	76.4	-----	17.4	-----	12.1	11.7	-----
Maks.	11.7	28.7	19.2	23.6	50.3	104.	135.	42.4	35.3	33.1	12.1	27.2
Min.	11.2	9.44	11.7	12.6	16.1	36.0	33.8	16.8	8.60	10.3	9.02	9.44
Ortalama	11.4	14.2	13.4	15.8	31.1	58.5	62.5	24.9	15.3	14.1	11.8	11.5
LT/SN/Km2	3.80	4.76	4.48	5.26	10.4	19.5	20.9	8.32	5.09	4.71	3.94	3.83
AKIM mm.	10.2	12.3	12.0	14.1	25.1	52.3	54.1	22.3	13.2	12.6	10.6	9.94
MİL. M3	30.5	36.9	35.9	42.2	75.1	157.	162.	66.8	39.5	37.8	31.6	29.7

SU YILI (2006) YILLIK TOPLAM AKIM 745.00 MİLYON M3 249 MM. 7.9 LT/SN/Km2

17. Dogu Akdeniz Havzasi

D17A017 Göksu N. Gördürüp Köp.

YERİ : **BOZKIR SÖĞÜT BELDESİ**
32°18'27" Doğu - 37°6'49" Kuzey

YAĞIŞ ALANI : **364,00 km2** **YAKLAŞIK KOT : 1241 m**

GÖZLEM SÜRESİ : **01.08.1967 - 30.09.2006**

ORTALAMA AKIMLAR : **Gözlem süresinde 3.964 m3/sn. (38 Yıllık) 2006 Su yılında 4.839 m3/sn.**

ANLIK EN ÇOK VE EN AZ AKIMLAR:

2006 Su yılında anlık ençok akım	**:**	**51.0**	**m3/sn**	**17.04.2006**
2006 Su yılında anlık enaz akım	**:**	**0.048**	**m3/sn**	**31.07.2006**
Gözlem süresinde anlık ençok akım	**:**	**238.**	**m3/sn**	**06.03.2004**
Gözlem süresinde anlık enaz akım	**:**	**0.000**	**m3/sn**	**17.09.1983**

İstasyon için kullanılmış anahtar bulunamadı.

Akımlar 01 Ekim 2005 'den 30 Eylül 2006' a kadar m3/sn olarak

Gün	Ekim	Kasım	Aralık	Ocak	Şubat	Mart	Nisan	Mayıs	Haziran	Temmuz	Ağustos	Eylül
01	0.245	0.245	2.10	1.16	2.50	10.2	22.0	12.2	2.90	0.690	0.177	0.107
02	0.245	0.245	2.28	1.16	2.50	13.1	25.9	12.5	2.90	0.640	0.177	0.107
03	0.245	0.245	1.64	1.16	2.70	14.6	24.0	11.9	2.50	0.590	0.177	0.107
04	0.245	0.601	1.80	1.42	3.10	17.8	21.8	11.6	2.50	0.540	0.177	0.107
05	0.245	0.601	1.95	1.42	3.48	16.1	19.3	11.0	2.15	0.490	0.177	0.107
06	0.245	0.601	1.64	1.55	4.20	14.3	20.0	10.5	2.15	0.450	0.149	0.107
07	0.245	0.601	1.34	2.00	6.14	14.6	22.3	9.11	1.85	0.410	0.149	0.107
08	0.245	0.601	1.10	2.50	5.87	14.0	25.3	9.65	1.70	0.370	0.149	0.107
09	0.245	0.601	0.735	2.30	4.76	11.9	25.3	8.57	1.55	0.370	0.149	0.107
10	0.245	0.601	0.856	2.30	4.76	9.65	24.3	7.76	1.42	0.370	0.149	0.107
11	0.245	0.601	0.735	2.30	6.41	8.84	23.6	8.03	1.55	0.330	0.149	0.107
12	0.245	0.601	0.625	2.30	7.22	8.57	25.3	8.57	0.944	0.330	0.149	0.107
13	0.245	0.601	0.625	2.15	6.95	9.11	27.9	8.84	1.08	0.330	0.149	0.107
14	0.245	0.601	0.625	2.15	5.60	10.2	30.8	8.84	1.01	0.290	0.149	0.107
15	0.245	0.601	0.625	2.00	4.48	9.92	36.6	8.30	0.944	0.290	0.149	0.107
16	0.245	0.601	0.625	2.00	3.84	9.92	50.0	7.49	0.944	0.262	0.127	0.127
17	0.245	0.601	0.856	2.15	3.66	8.84	46.8	6.41	0.876	0.262	0.127	0.127
18	0.245	0.601	1.22	2.00	3.48	8.57	30.8	6.14	0.876	0.262	0.127	0.127
19	0.245	0.601	3.18	2.70	3.84	9.11	24.0	6.41	0.808	0.262	0.127	0.127
20	0.245	1.06	3.84	5.32	4.76	9.65	25.6	6.14	0.808	0.234	0.127	0.127
21	0.245	5.00	3.30	3.30	4.48	10.7	23.3	6.14	0.740	0.234	0.127	0.127
22	0.245	4.56	2.15	2.90	4.76	14.0	19.3	5.87	0.740	0.234	0.127	0.127
23	0.245	3.18	1.85	3.30	6.41	18.0	18.3	6.14	0.740	0.234	0.127	0.127
24	0.245	2.10	1.70	3.66	7.76	24.3	17.0	6.14	0.740	0.234	0.127	0.127
25	0.245	1.64	1.55	3.48	9.11	24.9	13.7	5.60	0.690	0.234	0.127	0.127
26	0.245	1.10	1.16	3.10	11.0	20.3	11.6	5.04	0.690	0.205	0.127	0.127
27	0.245	0.977	1.16	2.90	11.3	20.0	10.7	4.76	0.690	0.205	0.127	0.127
28	0.245	1.64	1.29	2.50	10.2	20.5	11.3	4.20	0.690	0.205	0.127	0.127
29	0.245	2.46	1.16	2.30	-----	21.5	12.2	4.02	0.690	0.205	0.127	0.127
30	0.245	3.36	1.16	2.50	-----	23.0	13.1	3.66	0.640	0.177	0.127	0.127
31	0.245	-----	1.16	2.50	-----	25.6	-----	3.48	-----	0.177	0.127	-----
Maks.	0.245	5.44	4.02	6.41	11.6	26.9	51.0	13.1	2.90	0.690	0.177	0.127
Min.	0.245	0.245	0.625	1.16	2.50	8.30	10.5	3.48	0.640	0.048	0.127	0.107
Ortalama	0.245	1.25	1.49	2.40	5.55	14.6	23.4	7.58	1.28	0.326	0.142	0.117
LT/SN/Km2	0.673	3.43	4.08	6.60	15.2	40.0	64.3	20.8	3.53	0.896	0.391	0.321
AKIM mm.	1.80	8.88	10.9	17.7	36.9	107.	167.	55.8	9.14	2.40	1.05	0.833
MİL. M3	0.656	3.23	3.98	6.44	13.4	39.0	60.7	20.3	3.33	0.874	0.381	0.303

SU YILI (2006) YILLIK TOPLAM AKIM 152.59 MİLYON M3 419 MM. 13.3 LT/SN/Km2

17. Dogu Akdeniz Havzasi

D17A024 KORUCAK D. ÇATALDEĞİRMEN

YERİ : **OVACIK-ANAMUR YOLUNUN 22.KM SİNDE SAĞA AYRILAN KOCAŞLI-GÜLNAR YOLUNUN 9.KM.SİNDEKİ KÖPRÜNÜN 200M MANSABINDADIR.**
33°32'12" Doğu - 36°14'12" Kuzey

YAĞIŞ ALANI : **194,00 km2** **YAKLAŞIK KOT : 160 m**

GÖZLEM SÜRESİ : **17.11.1976 - 30.09.2006**

ORTALAMA AKIMLAR : **Gözlem süresinde 1.206 m3/sn. (29 Yıllık) 2006 Su yılında 0.701 m3/sn.**

ANLIK EN ÇOK VE EN AZ AKIMLAR:

2006 Su yılında anlık ençok akım	:	**22.9**	**m3/sn**	**11.02.2006**
2006 Su yılında anlık enaz akım	:	**0.003**	**m3/sn**	**30.12.2005**
Gözlem süresinde anlık ençok akım	:	**130.**	**m3/sn**	**23.02.1978**
Gözlem süresinde anlık enaz akım	:	**0.000**	**m3/sn**	**26.07.1977**

9. Anahtar Eğrisi (Seviyeler cm olarak)

Seviye	Akım	Seviye	Akım	Seviye	Akım	Seviye	Akım
1	0.000	31	2.7	131	38.0	251	72.0
5	0.000	51	9.4	151	44.0	291	82.0
9	0.007	71	16.6	171	50.0	301	84.0
13	0.080	91	24.0	191	55.0	351	94.0
17	0.281	111	31.0	211	60.0		

Akımlar 01 Ekim 2005 'den 30 Eylül 2006' a kadar m3/sn olarak

Gün	Ekim	Kasım	Aralık	Ocak	Şubat	Mart	Nisan	Mayıs	Haziran	Temmuz	Ağustos	Eylül
01	0.080	0.160	0.281	0.210	0.479	1.08	0.721	0.210	0.160	0.052	0.031	0.003
02	0.118	0.160	0.281	0.210	0.358	1.26	0.600	0.210	0.160	0.080	0.031	0.007
03	0.118	0.160	0.281	0.210	0.358	0.901	0.600	0.281	0.160	0.160	0.031	0.007
04	0.052	0.160	0.281	0.210	0.358	0.901	0.600	0.600	0.160	0.160	0.031	0.017
05	0.052	0.160	0.281	0.210	0.358	0.901	0.600	0.281	0.118	0.160	0.017	0.017
06	0.052	0.160	0.281	0.210	0.600	0.901	0.600	0.281	0.080	0.160	0.007	0.017
07	0.052	0.160	0.281	0.210	4.81	0.721	0.479	0.358	0.080	0.118	0.017	0.017
08	0.052	0.160	0.281	0.210	10.2	0.721	0.479	0.281	0.118	0.118	0.031	0.017
09	0.052	0.160	0.281	0.160	12.4	2.05	0.358	0.281	0.160	0.080	0.031	0.017
10	0.052	0.210	0.281	0.160	9.40	1.44	0.358	0.281	0.160	0.080	0.031	0.007
11	0.052	0.210	0.281	0.160	16.3	1.44	0.281	0.281	0.118	0.080	0.017	0.007
12	0.080	0.210	0.281	0.160	14.5	1.26	0.281	0.281	0.118	0.052	0.007	0.007
13	0.080	0.210	0.281	0.160	12.4	1.08	0.281	0.210	0.118	0.052	0.007	0.007
14	0.080	0.210	0.281	0.160	8.11	1.62	0.281	0.210	0.118	0.052	0.031	0.007
15	0.080	0.210	0.281	0.160	5.84	2.27	0.281	0.210	0.118	0.052	0.031	0.007
16	0.118	0.210	0.358	0.160	4.13	1.84	0.281	0.210	0.118	0.052	0.031	0.007
17	0.160	0.210	0.358	0.210	3.56	1.62	0.281	0.210	0.118	0.052	0.031	0.007
18	0.160	0.210	2.05	9.40	2.70	1.84	0.281	0.210	0.118	0.052	0.031	0.007
19	0.160	0.281	4.13	9.40	2.48	1.62	0.281	0.210	0.080	0.052	0.031	0.017
20	0.160	0.358	1.62	3.27	2.27	1.44	0.281	0.160	0.080	0.052	0.031	0.017
21	0.160	0.358	0.600	0.281	2.05	1.44	0.281	0.160	0.080	0.052	0.031	0.031
22	0.160	0.281	0.281	0.210	1.62	1.26	0.281	0.160	0.080	0.052	0.031	0.031
23	0.160	0.281	0.281	0.281	1.62	1.26	0.281	0.210	0.080	0.080	0.031	0.031
24	0.160	0.281	0.281	0.281	1.62	1.26	0.281	0.160	0.118	0.080	0.031	0.080
25	0.160	0.281	0.281	3.84	1.62	1.08	0.281	0.160	0.118	0.080	0.031	1.62
26	0.160	0.281	0.281	4.47	1.44	1.08	0.281	0.160	0.118	0.052	0.031	0.160
27	0.160	0.281	0.281	2.05	1.26	1.08	0.281	0.160	0.118	0.052	0.031	0.160
28	0.160	0.281	0.281	1.26	1.26	0.901	0.281	0.160	0.080	0.031	0.017	0.160
29	0.160	0.281	0.281	0.721	-----	0.721	0.281	0.160	0.210	0.031	0.007	0.160
30	0.160	0.281	0.160	0.479	-----	0.721	0.281	0.160	0.080	0.031	0.007	0.160
31	0.160	-----	0.160	0.479	-----	0.721	-----	0.160	-----	0.031	0.007	-----
Maks.	0.160	0.479	21.8	11.7	22.9	2.99	0.721	0.901	6.97	0.358	0.031	5.50
Min.	0.031	0.160	0.003	0.160	0.358	0.721	0.281	0.160	0.052	0.031	0.003	0.003
Ortalama	0.115	0.229	0.513	1.28	4.43	1.24	0.367	0.228	0.118	0.074	0.025	0.094
LT/SN/Km2	0.594	1.18	2.64	6.58	22.8	6.39	1.89	1.17	0.609	0.380	0.127	0.483
AKIM mm.	1.59	3.05	7.08	17.6	55.3	17.1	4.91	3.15	1.58	1.02	0.339	1.25
MİL. M3	0.308	0.592	1.37	3.42	10.7	3.32	0.952	0.611	0.306	0.198	0.066	0.243

SU YILI (2006) YILLIK TOPLAM AKIM 22.09 MİLYON M3 114 MM. 3.6 LT/SN/Km2

17. Dogu Akdeniz Havzasi

D17A027 BIÇKICI D. İNCEĞİZ

YERİ : **GAZİPAŞA İLÇESİNDEKİ OTOBÜS GARAJI YANINDAN GEÇEN YAYLA YOLUNU TAKİBEN 6 KM.SONRA SOLA SAPILARAK SULAMA KANALINI TAKRİBEN 3 KM. SONRA İSTASYONA VARILIR. 32°21'15" Doğu - 36°19'34" Kuzey**

YAĞIŞ ALANI : **134,00 km2** **YAKLAŞIK KOT : 60 m**

GÖZLEM SÜRESİ : **22.10.1978 - 30.09.2006**

ORTALAMA AKIMLAR : **Gözlem süresinde 4.113 m3/sn. (21 Yıllık) 2006 Su yılında 3.822 m3/sn.**

ANLIK EN ÇOK VE EN AZ AKIMLAR:

2006 Su yılında anlık ençok akım	**:**	**53.5**	**m3/sn**	**18.12.2005**
2006 Su yılında anlık enaz akım	**:**	**0.000**	**m3/sn**	**01.10.2005**
Gözlem süresinde anlık ençok akım	**:**	**540.**	**m3/sn**	**21.11.2001**
Gözlem süresinde anlık enaz akım	**:**	**0.000**	**m3/sn**	**05.10.1979**

Akımlar 01 Ekim 2005 'den 30 Eylül 2006' a kadar m3/sn olarak

Gün	Ekim	Kasım	Aralık	Ocak	Şubat	Mart	Nisan	Mayıs	Haziran	Temmuz	Ağustos	Eylül
01	KURU	0.139	0.670	1.53	3.24	5.68	13.7	4.36	0.820	0.139	0.038	KURU
02	KURU	0.200	0.670	1.35	2.96	6.16	15.6	4.08	0.820	0.119	0.033	KURU
03	KURU	0.200	0.670	1.35	2.96	6.16	15.6	4.08	0.740	0.099	0.024	KURU
04	KURU	3.52	0.670	1.35	2.68	6.64	14.3	3.52	0.670	0.079	0.014	KURU
05	KURU	1.53	0.530	1.35	2.40	7.12	13.1	2.96	0.670	0.350	0.012	KURU
06	KURU	1.01	0.305	1.53	3.24	6.16	12.5	2.68	0.530	0.900	0.009	KURU
07	KURU	0.670	0.305	1.88	21.9	6.16	12.5	2.40	0.405	0.600	KURU	KURU
08	KURU	0.460	0.305	1.70	25.9	9.04	12.5	2.40	0.405	0.230	KURU	KURU
09	KURU	0.350	0.305	1.70	23.6	15.0	12.5	2.23	0.350	0.200	KURU	KURU
10	KURU	0.350	0.305	1.53	24.7	10.6	13.1	2.05	0.260	0.160	KURU	KURU
11	KURU	0.305	0.305	1.35	30.3	8.56	13.1	1.88	0.260	0.139	KURU	KURU
12	KURU	0.305	0.305	1.35	24.7	7.12	13.1	1.88	0.200	0.119	KURU	KURU
13	KURU	0.260	0.305	1.24	20.2	7.60	13.1	1.70	0.200	0.119	KURU	KURU
14	KURU	0.260	0.305	1.13	15.0	17.9	14.3	1.70	0.180	0.099	KURU	KURU
15	KURU	0.260	0.350	1.13	10.6	23.6	15.6	1.53	0.180	0.099	KURU	KURU
16	0.009	0.200	0.350	0.900	8.56	16.8	21.9	1.35	0.160	0.099	KURU	KURU
17	9.52	0.160	1.13	0.900	6.64	13.7	19.6	1.35	0.160	0.079	KURU	KURU
18	0.350	0.305	16.8	0.820	5.68	12.5	15.0	1.35	0.160	0.079	KURU	KURU
19	0.350	1.53	21.3	0.900	5.68	25.9	13.1	1.24	0.160	0.079	KURU	KURU
20	0.350	7.12	19.0	10.0	5.20	20.2	12.5	1.13	0.139	0.079	KURU	KURU
21	0.200	6.64	10.0	4.08	4.92	17.3	11.2	1.01	0.139	0.058	KURU	KURU
22	0.160	2.96	6.16	2.23	4.92	16.2	9.52	0.900	0.139	0.058	KURU	KURU
23	0.119	1.70	4.64	2.68	4.92	16.2	9.04	0.900	0.119	0.058	KURU	KURU
24	0.099	1.24	4.08	3.52	4.92	17.3	8.08	1.01	0.119	0.058	KURU	KURU
25	0.099	0.900	3.52	16.2	4.92	20.7	7.60	1.01	0.119	0.058	KURU	KURU
26	0.099	0.820	2.68	18.5	5.68	17.9	6.16	1.13	0.180	0.058	KURU	0.007
27	0.099	0.740	2.23	10.0	5.68	16.2	5.68	1.01	0.180	0.058	KURU	0.230
28	0.099	0.740	2.05	6.64	5.20	15.0	4.92	0.900	0.260	0.058	KURU	0.200
29	0.160	0.670	1.88	4.92	-----	15.0	4.92	0.900	0.200	0.058	KURU	0.180
30	0.139	0.670	1.70	4.08	-----	14.3	4.64	0.900	0.180	0.038	KURU	0.180
31	0.099	-----	1.70	3.80	-----	14.3	-----	0.820	-----	0.058	KURU	-----
Maks.	25.9	20.7	53.5	40.9	48.8	38.2	26.4	4.64	2.40	7.60	0.038	0.600
Min.	KURU	0.038	0.180	0.820	2.40	5.20	4.36	0.820	0.119	0.033	KURU	KURU
Ortalama	0.386	1.21	3.40	3.60	10.3	13.3	11.9	1.82	0.303	0.145	0.004	0.027
LT/SN/Km2	2.88	9.01	25.4	26.9	76.6	99.4	89.2	13.6	2.26	1.08	0.031	0.198
AKIM mm.	7.71	23.3	68.0	72.0	185.	266.	231.	36.3	5.87	2.89	0.084	0.514
MİL. M3	1.03	3.13	9.12	9.65	24.8	35.7	31.0	4.87	0.787	0.387	0.011	0.069

SU YILI (2006) YILLIK TOPLAM AKIM 120.55 MİLYON M3 900 MM. 28.5 LT/SN/Km2

17. Dogu Akdeniz Havzasi

D17A033 Göksu N. Aladag Köp.

YERİ : **HADİM YAĞCILAR KÖYÜ**
32°35'32" Doğu - 37°3'8" Kuzey

YAĞIŞ ALANI : **588,40 km2** **YAKLAŞIK KOT : 850 m**

GÖZLEM SÜRESİ : **01.12.1985 - 30.09.2006**

ORTALAMA AKIMLAR : **Gözlem süresinde 7.510 m3/sn. (19 Yıllık) 2006 Su yılında 5.371 m3/sn.**

ANLIK EN ÇOK VE EN AZ AKIMLAR:

2006 Su yılında anlık ençok akım	**:**	**53.6**	**m3/sn**	**16.04.2006**
2006 Su yılında anlık enaz akım	**:**	**0.009**	**m3/sn**	**12.08.2006**
Gözlem süresinde anlık ençok akım	**:**	**245.**	**m3/sn**	**05.03.2004**
Gözlem süresinde anlık enaz akım	**:**	**0.000**	**m3/sn**	**29.08.1997**

İstasyon için kullanılmış anahtar bulunamadı.

Akımlar 01 Ekim 2005 'den 30 Eylül 2006' a kadar m3/sn olarak

Gün	Ekim	Kasım	Aralık	Ocak	Şubat	Mart	Nisan	Mayıs	Haziran	Temmuz	Ağustos	Eylül
01	0.210	0.596	2.35	1.60	2.48	11.8	25.2	14.0	3.02	0.668	0.031	0.012
02	0.210	0.640	1.94	1.60	2.62	12.9	28.6	13.7	2.70	0.603	0.038	0.012
03	0.210	0.640	1.80	1.60	2.62	12.9	26.0	13.1	2.54	0.537	0.023	0.012
04	0.210	1.30	1.80	1.60	2.62	16.8	24.5	13.1	2.38	0.537	0.023	0.018
05	0.235	1.30	1.80	1.70	2.74	15.6	21.9	12.2	2.06	0.471	0.018	0.023
06	0.235	1.22	1.80	1.70	3.10	14.1	22.2	11.6	1.90	0.431	0.012	0.031
07	0.235	1.15	1.70	1.70	6.10	14.8	23.7	10.1	1.78	0.431	0.012	0.023
08	0.235	1.07	1.60	2.21	11.1	15.1	26.0	10.4	1.55	0.391	0.012	0.018
09	0.235	0.996	1.50	2.48	9.49	13.8	25.5	9.80	1.44	0.351	0.012	0.018
10	0.235	0.996	1.50	2.48	8.58	12.6	25.0	8.90	1.32	0.351	0.012	0.018
11	0.260	0.920	1.40	2.48	9.26	12.2	23.7	8.30	1.22	0.311	0.012	0.012
12	0.260	0.996	1.30	2.48	10.9	11.8	24.5	8.60	1.01	0.311	0.009	0.012
13	0.260	0.996	1.30	2.35	11.8	12.2	26.0	8.30	1.11	0.271	0.009	0.012
14	0.260	0.996	1.30	2.21	9.95	13.8	29.6	8.90	1.01	0.198	0.009	0.012
15	0.260	0.920	1.21	2.21	8.80	14.3	31.2	8.30	1.01	0.235	0.009	0.012
16	0.292	0.808	1.21	2.21	8.36	14.6	46.9	7.52	1.01	0.198	0.009	0.012
17	0.292	0.808	1.21	2.21	7.92	13.8	46.6	6.80	0.800	0.198	0.009	0.012
18	0.292	0.808	1.12	2.21	7.70	13.6	32.2	6.32	0.734	0.198	0.009	0.012
19	0.292	1.93	1.40	2.07	7.48	13.6	24.8	6.56	0.734	0.162	0.012	0.018
20	0.292	2.84	2.98	4.54	7.70	13.6	24.8	6.32	0.668	0.162	0.009	0.018
21	0.324	3.78	2.98	3.42	8.14	13.6	23.7	6.08	0.668	0.143	0.009	0.018
22	0.356	3.90	2.48	2.86	8.58	15.3	20.3	5.84	0.668	0.143	0.009	0.031
23	0.420	2.98	2.21	2.74	9.03	19.1	20.0	6.08	0.668	0.123	0.009	0.059
24	0.508	2.35	2.07	2.98	9.95	31.8	18.8	6.08	0.668	0.143	0.009	0.088
25	0.596	2.07	2.07	3.10	10.6	29.6	16.4	5.84	0.603	0.123	0.009	0.123
26	0.596	1.80	1.80	2.98	10.2	24.2	13.7	4.97	0.603	0.088	0.009	0.123
27	0.596	1.70	1.70	2.86	12.9	24.0	12.5	4.76	0.603	0.070	0.009	0.123
28	0.596	1.70	1.70	2.74	12.2	24.0	12.8	4.13	0.603	0.059	0.012	0.123
29	0.596	1.80	1.60	2.62	-----	24.7	13.1	3.92	0.603	0.070	0.018	0.123
30	0.596	2.35	1.60	2.62	-----	24.7	14.6	3.50	0.668	0.070	0.012	0.088
31	0.596	-----	1.60	2.48	-----	28.3	-----	3.34	-----	0.059	0.012	-----
Maks.	0.596	4.46	3.10	5.90	12.9	34.7	53.6	15.2	3.18	0.668	0.047	0.143
Min.	0.210	0.596	1.12	1.60	2.48	11.8	11.9	3.18	0.603	0.023	0.009	0.012
Ortalama	0.348	1.55	1.74	2.42	7.96	17.2	24.2	7.98	1.21	0.261	0.013	0.041
LT/SN/Km2	0.592	2.63	2.96	4.11	13.5	29.2	41.1	13.6	2.06	0.444	0.022	0.069
AKIM mm.	1.58	6.81	7.93	11.0	32.7	78.3	106.	36.3	5.34	1.19	0.060	0.179
MİL. M3	0.932	4.01	4.67	6.48	19.3	46.1	62.6	21.4	3.14	0.700	0.035	0.105

SU YILI (2006) YILLIK TOPLAM AKIM 169.47 MİLYON M3 288 MM. 9.1 LT/SN/Km2

17. Dogu Akdeniz Havzasi

D17A034 Bogaz D. Sazak Köp.

YERİ : **HADİM SAZAK KÖYÜ**
32°31'58" Doğu - 36°57'3" Kuzey

YAĞIŞ ALANI : **68,00 km2** **YAKLAŞIK KOT : 1075 m**

GÖZLEM SÜRESİ : **01.12.1985 - 30.09.2006**

ORTALAMA AKIMLAR : **Gözlem süresinde 1.210 m3/sn. (18 Yıllık) 2006 Su yılında 1.057 m3/sn.**

ANLIK EN ÇOK VE EN AZ AKIMLAR:

2006 Su yılında anlık ençok akım	**:**	**9.70**	**m3/sn**	**30.03.2006**
2006 Su yılında anlık enaz akım	**:**	**0.000**	**m3/sn**	**18.10.2005**
Gözlem süresinde anlık ençok akım	**:**	**88.8**	**m3/sn**	**05.03.2004**
Gözlem süresinde anlık enaz akım	**:**	**0.000**	**m3/sn**	**01.10.1999**

İstasyon için kullanılmış anahtar bulunamadı.

Akımlar 01 Ekim 2005 'den 30 Eylül 2006' a kadar m3/sn olarak

Gün	Ekim	Kasım	Aralık	Ocak	Şubat	Mart	Nisan	Mayıs	Haziran	Temmuz	Ağustos	Eylül
01	KURU	KURU	0.599	0.124	0.137	1.99	8.35	2.12	0.073	0.035	0.035	0.035
02	KURU	KURU	0.536	0.124	0.226	2.51	8.62	1.99	0.060	0.035	0.035	0.035
03	KURU	KURU	0.536	0.150	0.264	2.77	8.08	1.99	0.048	0.035	0.035	0.035
04	KURU	0.060	0.536	0.188	0.340	3.03	8.08	1.86	0.048	0.035	0.035	0.035
05	KURU	0.048	0.536	0.188	0.378	3.03	7.54	1.73	0.048	0.035	0.035	0.035
06	KURU	0.048	0.473	0.188	0.416	2.77	7.81	1.60	0.048	0.035	0.035	0.035
07	KURU	0.048	0.473	0.264	0.492	3.03	8.08	1.60	0.048	0.035	0.035	0.035
08	KURU	0.048	0.473	0.340	0.492	3.03	8.35	1.49	0.048	0.035	0.035	0.035
09	KURU	0.048	0.410	0.340	0.454	2.64	8.35	1.49	0.048	0.035	0.035	0.035
10	KURU	0.048	0.410	0.340	0.454	2.38	8.35	1.39	0.035	0.035	0.035	0.035
11	KURU	0.060	0.347	0.340	0.637	2.12	8.08	1.17	0.035	0.035	0.035	0.035
12	KURU	0.060	0.313	0.302	0.851	2.12	8.35	0.958	0.035	0.035	0.035	0.035
13	KURU	0.060	0.279	0.302	0.851	2.25	8.89	0.851	0.035	0.035	0.035	0.035
14	KURU	0.060	0.244	0.264	0.637	2.12	9.70	0.744	0.035	0.035	0.035	0.035
15	KURU	0.060	0.210	0.264	0.492	1.86	9.43	0.637	0.035	0.035	0.035	0.035
16	KURU	0.060	0.210	0.226	0.454	1.86	7.98	0.530	0.035	0.035	0.035	0.035
17	KURU	0.060	0.210	0.226	0.454	1.86	7.44	0.492	0.035	0.035	0.035	0.035
18	KURU	0.086	0.210	0.264	0.454	1.86	5.55	0.416	0.035	0.035	0.035	0.035
19	KURU	0.492	0.830	0.302	0.492	1.86	4.20	0.378	0.035	0.035	0.035	0.035
20	KURU	1.86	0.264	0.340	0.530	1.99	4.74	0.340	0.035	0.035	0.035	0.035
21	KURU	3.65	0.226	0.264	0.637	2.25	4.07	0.302	0.035	0.035	0.035	0.035
22	KURU	2.22	0.188	0.226	0.637	2.90	3.68	0.264	0.035	0.035	0.035	0.035
23	KURU	1.86	0.150	0.226	0.958	3.55	3.42	0.226	0.035	0.035	0.035	0.035
24	KURU	1.62	0.137	0.226	1.28	8.08	3.29	0.188	0.035	0.035	0.035	0.035
25	KURU	1.08	0.112	0.226	1.86	7.54	2.77	0.150	0.035	0.035	0.035	0.035
26	KURU	0.830	0.099	0.226	2.12	7.00	2.25	0.150	0.035	0.035	0.035	0.035
27	KURU	0.746	0.086	0.226	2.12	7.27	1.99	0.124	0.035	0.035	0.035	0.035
28	KURU	0.599	0.073	0.188	1.86	7.54	1.99	0.124	0.035	0.035	0.035	0.035
29	KURU	0.599	0.099	0.188	-----	7.27	2.12	0.099	0.035	0.035	0.035	0.035
30	KURU	0.746	0.137	0.124	-----	7.81	2.25	0.073	0.035	0.035	0.035	0.035
31	KURU	-----	0.124	0.099	-----	8.62	-----	0.099	-----	0.035	0.035	-----
Maks.	KURU	5.08	1.16	0.378	2.77	9.70	9.70	2.38	0.099	0.035	0.035	0.035
Min.	KURU	KURU	0.073	0.086	0.124	1.86	1.86	0.073	0.035	0.035	0.035	0.035
Ortalama	KURU	0.572	0.307	0.235	0.749	3.77	6.13	0.825	0.040	0.035	0.035	0.035
LT/SN/Km2	0.000	8.41	4.52	3.46	11.0	55.5	90.1	12.1	0.590	0.515	0.515	0.515
AKIM mm.	0.000	21.8	12.1	9.27	26.7	149.	234.	32.5	1.53	1.38	1.38	1.33
MİL. M3	0.000	1.48	0.823	0.630	1.81	10.1	15.9	2.21	0.104	0.094	0.094	0.091

SU YILI (2006) YILLIK TOPLAM AKIM 33.34 MİLYON M3 490 MM. 15.5 LT/SN/Km2

17. Dogu Akdeniz Havzasi

D17A035 Ilicapinar D. Korucu Köp.

YERİ : **HADİM SAZAK KÖYÜ**
32°31'51" Doğu - 36°57'42" Kuzey

YAĞIŞ ALANI : **491,00 km2** **YAKLAŞIK KOT : 925 m**

GÖZLEM SÜRESİ : **01.12.1985 - 30.09.2006**

ORTALAMA AKIMLAR : **Gözlem süresinde 5.589 m3/sn. (17 Yıllık) 2006 Su yılında 3.974 m3/sn.**

ANLIK EN ÇOK VE EN AZ AKIMLAR:

2006 Su yılında anlık ençok akım	**:**	**29.5**	**m3/sn**	**15.04.2006**
2006 Su yılında anlık enaz akım	**:**	**0.000**	**m3/sn**	**14.08.2006**
Gözlem süresinde anlık ençok akım	**:**	**225.**	**m3/sn**	**28.12.2001**
Gözlem süresinde anlık enaz akım	**:**	**0.000**	**m3/sn**	**31.07.1986**

İstasyon için kullanılmış anahtar bulunamadı.

Akımlar 01 Ekim 2005 'den 30 Eylül 2006' a kadar m3/sn olarak

Gün	Ekim	Kasım	Aralık	Ocak	Şubat	Mart	Nisan	Mayıs	Haziran	Temmuz	Ağustos	Eylül
01	0.096	0.096	1.18	0.960	1.20	11.3	24.0	7.36	1.02	0.630	0.091	KURU
02	0.073	0.143	1.18	0.960	1.84	12.8	25.2	7.07	0.941	0.535	0.091	KURU
03	0.073	0.174	1.18	1.02	2.08	13.6	24.0	7.66	0.879	0.488	0.091	KURU
04	0.073	0.721	1.10	1.20	2.65	14.3	22.0	7.36	0.879	0.440	0.091	KURU
05	0.096	0.612	1.02	1.20	2.98	14.3	20.8	6.48	0.817	0.440	0.091	KURU
06	0.096	0.558	1.02	1.20	3.37	13.6	21.2	5.89	0.817	0.488	0.091	KURU
07	0.096	0.558	0.879	1.30	4.14	14.3	22.4	5.37	0.754	0.393	0.091	KURU
08	0.096	0.612	0.879	1.72	4.14	14.3	22.8	5.37	0.754	0.393	0.091	KURU
09	0.096	0.558	0.817	1.60	3.76	12.8	22.8	4.92	0.754	0.352	0.091	KURU
10	0.096	0.503	0.817	1.48	3.76	12.1	22.0	4.70	0.754	0.308	0.091	KURU
11	0.096	0.407	0.754	1.39	4.96	11.3	20.4	4.25	0.754	0.160	0.091	KURU
12	0.096	0.407	0.692	1.39	5.43	11.3	21.2	4.25	0.754	0.194	0.091	KURU
13	0.118	0.407	0.692	1.39	5.43	11.7	22.4	4.03	0.754	0.194	0.057	KURU
14	0.118	0.365	0.630	1.39	4.96	12.5	23.2	4.03	0.754	0.230	KURU	KURU
15	0.118	0.407	0.630	1.30	4.53	11.7	22.8	3.81	0.754	0.230	KURU	KURU
16	0.143	0.449	0.692	1.11	4.14	11.3	27.3	3.36	0.754	0.194	KURU	KURU
17	0.174	0.449	0.692	1.11	4.14	10.3	23.2	3.36	0.692	0.194	KURU	KURU
18	0.206	0.558	0.630	1.11	4.14	10.3	18.6	3.02	0.692	0.194	KURU	KURU
19	0.206	2.22	2.51	1.20	4.53	10.6	16.3	2.85	0.692	0.160	KURU	KURU
20	0.206	7.36	3.36	1.20	4.96	11.3	16.7	2.68	0.630	0.160	KURU	KURU
21	0.206	6.77	1.96	1.20	5.43	12.8	14.9	2.38	0.630	0.160	KURU	0.091
22	0.206	3.81	1.60	1.20	5.43	17.3	13.2	2.25	0.630	0.160	KURU	0.124
23	0.206	3.02	1.48	1.20	6.62	21.6	12.5	1.87	0.583	0.160	KURU	0.124
24	0.206	2.51	1.30	1.20	8.14	27.8	11.8	1.66	0.583	0.124	KURU	0.160
25	0.206	1.87	1.30	1.20	11.0	25.2	10.8	1.66	0.535	0.124	KURU	0.160
26	0.206	1.55	1.30	1.20	11.7	23.6	8.25	1.55	0.535	0.091	KURU	0.160
27	0.206	1.34	1.11	1.20	11.7	23.6	7.36	1.34	0.488	0.091	KURU	0.160
28	0.206	1.26	1.02	1.11	11.0	23.6	7.66	1.34	0.440	0.091	KURU	0.160
29	0.143	1.26	1.02	1.11	-----	23.6	7.95	1.26	0.440	0.091	KURU	0.160
30	0.096	1.26	0.960	0.900	-----	24.4	7.95	1.18	0.941	0.091	KURU	0.160
31	0.096	-----	0.960	0.781	-----	24.8	-----	1.10	-----	0.091	KURU	-----
Maks.	0.239	10.5	4.70	2.08	11.7	29.1	29.5	8.54	2.13	0.754	0.091	0.194
Min.	0.073	0.096	0.535	0.781	1.20	10.3	7.07	1.02	0.440	0.091	KURU	KURU
Ortalama	0.140	1.41	1.14	1.21	5.29	15.9	18.1	3.72	0.713	0.247	0.037	0.049
LT/SN/Km2	0.286	2.87	2.32	2.47	10.8	32.5	36.8	7.58	1.45	0.503	0.075	0.099
AKIM mm.	0.766	7.43	6.22	6.60	26.1	86.9	95.3	20.3	3.77	1.35	0.202	0.257
MİL. M3	0.376	3.65	3.06	3.24	12.8	42.7	46.8	9.97	1.85	0.661	0.099	0.126

SU YILI (2006) YILLIK TOPLAM AKIM 125.33 MİLYON M3 255 MM. 8.1 LT/SN/Km2

17. Dogu Akdeniz Havzasi

D17A037 Kaplança D. Dagli Köyü

YERİ : ERDEMLİ SORGUN YOLU 15.KM SINDEN SAGA AYRILAN ORMAN YOLUNDAN İTİBAREN 3.KM DEKİ KARGICAK BARAJI AKS YERİNDE
34°16'31" Doğu - 36°41'23" Kuzey

YAĞIŞ ALANI : 42 km2 YAKLAŞIK KOT : 325 m

GÖZLEM SÜRESİ : 01.10.1986 - 30.09.2006

ORTALAMA AKIMLAR : Gözlem süresinde 0.117 m3/sn. (17 Yıllık) 2006 Su yılında 0.034 m3/sn.

ANLIK EN ÇOK VE EN AZ AKIMLAR:

2006 Su yılında anlık ençok akım	:	0.280	m3/sn	08.03.2006
2006 Su yılında anlık enaz akım	:	0.000	m3/sn	01.10.2005
Gözlem süresinde anlık ençok akım	:	21.3	m3/sn	14.02.1990
Gözlem süresinde anlık enaz akım	:	0.000	m3/sn	14.08.1987

3. Anahtar Eğrisi (Seviyeler cm olarak)

Seviye	Akım	Seviye	Akım	Seviye	Akım	Seviye	Akım
150	0.700	200	10.7	280	38.3	360	72.0
160	1.6	210	13.6	300	46.3	370	77.0
170	3.2	220	17.0	320	54.4	380	82.0
180	5.4	240	24.0	340	63.0	390	87.0
190	8.0	260	31.0	350	67.5	400	92.0

Akımlar 01 Ekim 2005 'den 30 Eylül 2006' a kadar m3/sn olarak

Gün	Ekim	Kasım	Aralık	Ocak	Şubat	Mart	Nisan	Mayıs	Haziran	Temmuz	Ağustos	Eylül
01	KURU	KURU	KURU	0.042	0.042	0.076	0.120	0.006	KURU	KURU	KURU	KURU
02	KURU	KURU	KURU	0.042	0.042	0.076	0.120	0.006	KURU	KURU	KURU	KURU
03	KURU	KURU	KURU	0.028	0.042	0.076	0.100	0.006	KURU	KURU	KURU	KURU
04	KURU	KURU	KURU	0.028	0.028	0.076	0.100	0.002	KURU	KURU	KURU	KURU
05	KURU	KURU	KURU	0.028	0.028	0.076	0.120	0.018	KURU	0.180	KURU	KURU
06	KURU	KURU	KURU	0.028	0.028	0.076	0.100	0.042	KURU	0.156	KURU	KURU
07	KURU	KURU	KURU	0.028	0.076	0.076	0.100	0.042	KURU	0.120	KURU	KURU
08	KURU	KURU	KURU	0.028	0.120	0.100	0.100	0.018	KURU	0.120	KURU	KURU
09	KURU	KURU	KURU	0.060	0.120	0.100	0.100	0.018	KURU	0.120	KURU	KURU
10	KURU	KURU	KURU	0.060	0.156	0.076	0.100	0.011	KURU	0.120	KURU	KURU
11	KURU	KURU	KURU	0.060	0.156	0.076	0.100	0.011	KURU	0.120	KURU	KURU
12	KURU	KURU	KURU	0.060	0.156	0.076	0.100	0.011	KURU	0.120	KURU	KURU
13	KURU	KURU	KURU	0.076	0.156	0.076	0.100	0.011	KURU	0.120	KURU	KURU
14	KURU	KURU	0.006	0.100	0.156	0.076	0.076	0.011	KURU	0.120	KURU	KURU
15	KURU	KURU	0.076	0.100	0.156	0.076	0.076	0.006	KURU	0.120	KURU	KURU
16	KURU	KURU	0.076	0.100	0.156	0.120	0.076	0.002	KURU	0.120	KURU	KURU
17	KURU	KURU	0.076	0.028	0.156	0.120	0.076	0.002	KURU	0.120	KURU	KURU
18	KURU	KURU	0.076	0.011	0.120	0.120	0.060	0.002	KURU	0.006	KURU	KURU
19	KURU	KURU	0.076	0.011	0.120	0.120	0.060	0.002	KURU	KURU	KURU	KURU
20	KURU	KURU	0.076	0.018	0.120	0.120	0.060	0.002	KURU	KURU	KURU	KURU
21	KURU	KURU	0.076	0.018	0.120	0.100	0.060	0.002	KURU	KURU	KURU	KURU
22	KURU	KURU	0.076	0.018	0.100	0.100	0.060	0.002	KURU	KURU	KURU	KURU
23	KURU	KURU	0.076	0.018	0.100	0.100	0.060	KURU	KURU	KURU	KURU	0.018
24	KURU	KURU	0.060	0.028	0.100	0.120	0.060	KURU	KURU	KURU	KURU	0.018
25	KURU	KURU	0.060	0.042	0.100	0.120	0.011	KURU	KURU	KURU	KURU	0.018
26	KURU	KURU	0.060	0.042	0.100	0.120	0.006	KURU	KURU	KURU	KURU	0.018
27	KURU	KURU	0.060	0.042	0.100	0.120	0.006	KURU	KURU	KURU	KURU	0.018
28	KURU	KURU	0.042	0.042	0.100	0.120	0.006	KURU	KURU	KURU	KURU	0.018
29	KURU	KURU	0.042	0.042	-----	0.120	0.006	KURU	KURU	KURU	KURU	0.011
30	KURU	KURU	0.042	0.042	-----	0.120	0.006	KURU	KURU	KURU	KURU	0.011
31	KURU	-----	0.042	0.042	-----	0.120	-----	KURU	-----	KURU	KURU	-----
Maks.	KURU	KURU	0.076	0.156	0.180	0.280	0.120	0.060	KURU	0.280	KURU	0.028
Min.	KURU	KURU	KURU	0.006	0.028	KURU	0.002	KURU	KURU	KURU	KURU	KURU
Ortalama	KURU	KURU	0.035	0.042	0.106	0.098	0.071	0.008	KURU	0.054	KURU	0.004
LT/SN/Km2	0.000	0.000	0.000	0.000	0.000	0.000	0.000	0.000	0.000	0.000	0.000	0.000
AKIM mm.	0.000	0.000	0.000	0.000	0.000	0.000	0.000	0.000	0.000	0.000	0.000	0.000
MİL. M3	0.000	0.000	0.095	0.113	0.255	0.263	0.184	0.020	0.000	0.144	0.000	0.011

SU YILI (2006) YILLIK TOPLAM AKIM 1.08 MİLYON M3 0 MM. 0.0 LT/SN/Km2

17. Dogu Akdeniz Havzasi

D17A038 SEDRE Ç. KOCAOGLANLİ

YERİ : **ANTALYA-GAZİPAŞA YOLUNU TAKIBEN DEMIRTAŞ ILÇESINE VARILIR.5 KM.SONRA KOCAOĞLANLI MAHALLESINE VARILIR ANA YOLDAN SOLA SAPILARAK ISTASYONA VARILIR. 32°12'58" Doğu - 36°26'42" Kuzey**

YAĞIŞ ALANI : **158,00 km2** **YAKLAŞIK KOT : 35 m**

GÖZLEM SÜRESİ : **11.11.1987 - 30.09.2006**

ORTALAMA AKIMLAR : **Gözlem süresinde 2.850 m3/sn. (17 Yıllık) 2006 Su yılında 1.531 m3/sn.**

ANLIK EN ÇOK VE EN AZ AKIMLAR:

2006 Su yılında anlık ençok akım	**:**	**33.5**	**m3/sn**	**25.03.2006**
2006 Su yılında anlık enaz akım	**:**	**0.000**	**m3/sn**	**31.08.2006**
Gözlem süresinde anlık ençok akım	**:**	**299.**	**m3/sn**	**02.01.2002**
Gözlem süresinde anlık enaz akım	**:**	**0.000**	**m3/sn**	**29.08.1998**

Akımlar 01 Ekim 2005 'den 30 Eylül 2006' a kadar m3/sn olarak

Gün	Ekim	Kasım	Aralık	Ocak	Şubat	Mart	Nisan	Mayıs	Haziran	Temmuz	Ağustos	Eylül
01	0.106	0.178	0.476	0.612	1.72	2.44	4.78	1.58	0.339	0.270	0.082	0.046
02	0.106	0.270	0.476	0.544	1.58	2.44	4.78	1.58	0.339	0.202	0.082	0.046
03	0.130	0.270	0.476	0.544	1.58	2.44	4.47	1.44	0.407	0.178	0.082	0.005
04	0.130	0.818	0.407	0.612	1.44	2.44	4.16	1.44	0.339	0.178	0.082	0.001
05	0.106	0.886	0.407	0.612	1.44	2.44	3.69	1.44	0.339	0.270	0.082	0.021
06	0.106	0.612	0.407	0.612	1.72	2.28	3.54	1.44	0.339	0.544	0.082	0.021
07	0.106	0.476	0.407	0.612	7.42	2.14	3.38	1.30	0.339	0.476	0.082	0.021
08	0.082	0.339	0.407	0.681	19.2	2.91	3.22	1.30	0.339	0.476	0.082	0.034
09	0.082	0.339	0.407	0.681	11.1	6.64	3.22	1.30	0.339	0.407	0.082	0.034
10	0.082	0.339	0.339	0.681	12.6	4.47	3.22	1.30	0.339	0.339	0.082	0.021
11	0.106	0.339	0.339	0.681	15.7	3.54	3.07	1.16	0.270	0.270	0.082	0.021
12	0.058	0.270	0.339	0.681	11.6	3.22	3.07	1.03	0.270	0.202	0.058	KURU
13	0.058	0.270	0.339	0.612	8.81	3.22	3.07	1.03	0.270	0.202	0.058	0.001
14	0.058	0.202	0.339	0.544	6.33	7.42	2.91	1.03	0.202	0.178	0.058	0.009
15	0.058	0.178	0.339	0.544	5.09	10.7	3.07	0.886	0.202	0.178	0.058	0.009
16	0.106	0.178	0.407	0.544	3.85	7.42	3.85	0.886	0.202	0.154	0.046	0.021
17	0.130	0.178	0.681	0.544	3.38	6.33	3.54	0.818	0.202	0.130	0.046	0.021
18	0.178	0.202	3.22	0.544	3.07	6.02	2.91	0.818	0.178	0.130	0.046	0.021
19	0.202	0.544	4.78	0.544	2.91	12.6	2.59	0.818	0.178	0.130	0.058	0.009
20	0.178	0.818	4.16	3.07	2.91	8.81	2.59	0.818	0.154	0.082	0.058	KURU
21	0.178	1.58	2.28	2.59	2.91	6.95	2.44	0.749	0.154	0.082	0.046	0.005
22	0.154	1.03	1.44	1.72	2.91	6.33	2.28	0.681	0.130	0.082	0.046	0.046
23	0.154	0.749	1.16	1.58	2.91	6.02	2.28	0.544	0.130	0.106	0.034	0.178
24	0.178	0.612	1.03	1.86	2.75	6.33	2.00	0.544	0.130	0.106	0.046	0.202
25	0.154	0.612	0.818	5.71	2.75	11.1	1.86	0.612	0.154	0.058	0.046	0.270
26	0.154	0.544	0.749	9.28	2.75	7.88	1.72	0.612	0.154	0.058	0.034	0.270
27	0.130	0.544	0.749	4.16	2.59	7.42	1.72	0.612	0.154	0.082	0.021	0.270
28	0.130	0.544	0.612	3.07	2.59	7.42	1.58	0.612	0.178	0.082	0.034	0.202
29	0.130	0.476	0.612	2.44	-----	6.95	1.58	0.612	0.407	0.082	0.021	0.178
30	0.154	0.476	0.612	2.14	-----	6.33	1.58	0.407	0.339	0.058	0.021	0.178
31	0.178	-----	0.612	2.00	-----	5.71	-----	0.339	-----	0.082	0.009	-----
Maks.	0.202	1.72	6.95	13.1	32.0	33.5	4.78	1.58	0.749	0.749	0.106	0.476
Min.	0.034	0.178	0.339	0.544	1.30	2.14	1.58	0.178	0.058	0.009	KURU	KURU
Ortalama	0.125	0.496	0.962	1.65	5.20	5.75	2.94	0.959	0.251	0.189	0.056	0.072
LT/SN/Km2	0.788	3.14	6.09	10.4	32.9	36.4	18.6	6.07	1.59	1.20	0.356	0.456
AKIM mm.	2.11	8.13	16.3	27.9	79.6	97.5	48.2	16.3	4.11	3.21	0.955	1.18
MİL. M3	0.334	1.29	2.58	4.41	12.6	15.4	7.62	2.57	0.649	0.508	0.151	0.187

SU YILI (2006) YILLIK TOPLAM AKIM 48.30 MİLYON M3 306 MM. 9.7 LT/SN/Km2

17. Dogu Akdeniz Havzasi

D17A039 GÖKÇELER D. GAZİPASA

YERİ : **GAZİPAŞA ILÇESININ KORUBAŞI KÖPRÜSÜNDEN 1.5 KM. SONRA IST. VARILIR.**
32°22'32" Doğu - 36°17'20" Kuzey

YAĞIŞ ALANI : **139,40 km2** **YAKLAŞIK KOT : 56 m**

GÖZLEM SÜRESİ : **01.10.1990 - 30.09.2006**

ORTALAMA AKIMLAR : **Gözlem süresinde 2.626 m3/sn. (16 Yıllık) 2006 Su yılında 3.417 m3/sn.**

ANLIK EN ÇOK VE EN AZ AKIMLAR:

2006 Su yılında anlık ençok akım	:	**100.**	**m3/sn**	**10.02.2006**
2006 Su yılında anlık enaz akım	:	**0.000**	**m3/sn**	**13.10.2005**
Gözlem süresinde anlık ençok akım	:	**330.**	**m3/sn**	**08.03.1995**
Gözlem süresinde anlık enaz akım	:	**0.000**	**m3/sn**	**01.10.1990**

Akımlar 01 Ekim 2005 'den 30 Eylül 2006' a kadar m3/sn olarak

Gün	Ekim	Kasım	Aralık	Ocak	Şubat	Mart	Nisan	Mayıs	Haziran	Temmuz	Ağustos	Eylül
01	0.012	0.212	0.518	0.925	2.60	4.18	9.40	3.24	0.833	0.104	KURU	KURU
02	0.068	0.320	0.452	0.925	2.44	3.79	10.2	3.24	0.833	0.068	KURU	KURU
03	0.122	0.284	0.386	0.925	2.44	3.40	9.82	3.08	0.742	0.068	KURU	KURU
04	0.035	2.92	0.386	0.925	2.28	3.40	9.40	3.08	0.650	0.212	KURU	KURU
05	0.001	1.20	0.386	0.925	2.12	3.79	7.72	3.08	0.650	1.02	KURU	KURU
06	KURU	0.925	0.386	0.925	2.76	3.40	7.30	2.76	0.584	1.50	KURU	KURU
07	KURU	0.833	0.320	1.11	30.1	3.40	7.30	2.76	0.584	1.11	KURU	KURU
08	KURU	0.650	0.320	1.02	35.1	5.35	7.30	2.76	0.518	0.518	KURU	KURU
09	KURU	0.584	0.284	0.925	36.2	13.6	7.30	2.44	0.452	0.284	KURU	KURU
10	KURU	0.452	0.284	0.925	34.5	10.2	7.72	2.28	0.284	0.212	KURU	KURU
11	KURU	0.386	0.284	0.833	43.0	7.72	6.91	2.44	0.284	0.176	KURU	KURU
12	KURU	0.386	0.248	0.833	31.2	6.13	7.72	2.76	0.212	0.140	KURU	KURU
13	KURU	0.320	0.248	0.742	24.5	6.52	7.72	2.76	0.176	0.140	KURU	KURU
14	KURU	0.284	0.248	0.742	17.4	19.1	7.72	2.76	0.122	0.122	KURU	KURU
15	KURU	0.248	0.248	0.650	12.8	26.8	8.98	2.12	0.104	0.104	KURU	KURU
16	KURU	0.248	0.284	0.650	10.2	17.9	12.3	1.96	0.104	0.086	KURU	KURU
17	0.140	0.212	2.60	0.650	8.14	14.0	11.5	1.96	0.104	0.104	KURU	KURU
18	0.104	0.212	16.1	0.584	6.91	11.9	9.40	1.80	0.104	0.104	KURU	KURU
19	0.212	0.650	21.4	0.584	6.52	33.4	8.14	1.65	0.104	0.086	KURU	KURU
20	0.248	9.82	16.1	6.52	6.13	20.9	8.14	1.65	0.104	0.068	KURU	KURU
21	0.140	8.98	7.30	3.40	5.35	16.1	7.72	1.80	0.086	0.050	KURU	KURU
22	0.104	2.92	4.18	2.28	5.35	14.0	6.52	1.80	0.086	0.068	KURU	KURU
23	0.068	1.80	2.92	2.76	5.74	13.2	6.13	1.80	0.086	0.068	KURU	0.104
24	0.050	1.20	2.28	2.92	5.35	13.6	5.35	1.65	0.086	0.050	KURU	0.104
25	0.020	1.02	1.96	14.4	5.35	16.1	5.35	1.65	0.086	0.042	KURU	0.212
26	KURU	0.833	1.65	18.7	5.35	13.2	4.18	1.20	0.086	0.042	KURU	2.12
27	KURU	0.650	1.35	10.7	5.35	11.5	3.79	1.11	0.050	0.042	KURU	0.386
28	KURU	0.584	1.20	6.91	4.57	10.2	3.40	1.02	0.050	0.035	KURU	0.122
29	0.068	0.584	1.11	4.57	-----	10.2	3.40	1.02	0.035	0.035	KURU	0.068
30	0.452	0.584	1.11	3.24	-----	10.2	4.18	0.925	0.035	0.010	KURU	0.042
31	0.212	-----	1.02	2.92	-----	9.82	-----	0.925	-----	KURU	KURU	-----
Maks.	2.12	26.3	41.8	26.3	100.	50.2	15.7	5.35	0.925	5.35	KURU	21.4
Min.	KURU	0.140	0.140	0.584	2.12	3.24	3.24	0.925	0.027	KURU	KURU	KURU
Ortalama	0.066	1.34	2.82	3.07	12.8	11.5	7.40	2.11	0.274	0.215	KURU	0.105
LT/SN/Km2	0.476	9.64	20.3	22.0	92.2	82.6	53.1	15.2	1.97	1.54	0.000	0.755
AKIM mm.	1.27	25.0	54.3	59.0	223.	221.	138.	40.6	5.10	4.13	0.000	1.96
MİL. M3	0.178	3.48	7.57	8.22	31.1	30.8	19.2	5.66	0.711	0.576	0.000	0.273

SU YILI (2006) YILLIK TOPLAM AKIM 107.77 MİLYON M3 773 MM. 24.5 LT/SN/Km2

17. Dogu Akdeniz Havzasi

D17A040 ALATA Ç. SARILAR

YERİ : MERSİN İLİ ERDEMLİ İLÇESİ SARILAR KÖYÜ YAKININDADIR.
34°15'15" Doğu - 36°39'23" Kuzey

YAĞIŞ ALANI : 380,00 km2 YAKLAŞIK KOT : 125 m

GÖZLEM SÜRESİ : 01.10.1990 - 30.09.2006

ORTALAMA AKIMLAR : Gözlem süresinde 2.778 m3/sn. (16 Yıllık) 2006 Su yılında 1.367 m3/sn.

ANLIK EN ÇOK VE EN AZ AKIMLAR:

2006 Su yılında anlık ençok akım	:	14.3	m3/sn	14.03.2006
2006 Su yılında anlık enaz akım	:	0.087	m3/sn	07.07.2006
Gözlem süresinde anlık ençok akım	:	124.	m3/sn	15.12.1997
Gözlem süresinde anlık enaz akım	:	0.000	m3/sn	01.11.1993

5. Anahtar Eğrisi (Seviyeler cm olarak)

Seviye	Akım	Seviye	Akım	Seviye	Akım	Seviye	Akım
3	0.106	13	1.2	90	29.0	170	83.0
5	0.254	17	1.7	110	41.0	180	90.0
7	0.439	30	4.2	130	55.0	190	96.0
9	0.639	50	9.4	150	68.0	200	105.
11	0.897	70	17.5	160	76.0	230	132.

Akımlar 01 Ekim 2005 'den 30 Eylül 2006' a kadar m3/sn olarak

Gün	Ekim	Kasım	Aralık	Ocak	Şubat	Mart	Nisan	Mayıs	Haziran	Temmuz	Ağustos	Eylül
01	0.286	0.483	0.987	0.675	0.893	2.90	3.85	1.81	0.542	0.542	0.166	0.166
02	0.333	0.483	0.987	0.675	0.821	2.90	3.85	1.68	0.483	0.483	0.166	0.205
03	0.379	0.601	0.893	0.675	0.821	3.08	3.85	1.68	0.483	0.483	0.166	0.205
04	0.379	1.57	0.893	0.675	0.893	3.08	3.85	1.68	0.483	0.483	0.134	0.243
05	0.379	1.57	0.893	0.675	0.893	3.08	3.85	1.68	0.483	0.483	0.134	0.243
06	0.379	1.26	0.893	0.675	1.57	3.08	3.85	1.57	0.431	1.08	0.134	0.243
07	0.379	1.08	0.893	0.675	2.90	3.25	3.85	1.46	0.431	1.08	0.134	0.243
08	0.379	0.987	0.893	0.675	5.35	3.25	3.61	1.46	0.431	0.893	0.134	0.243
09	0.379	0.893	0.893	0.675	4.55	5.35	3.25	1.46	0.379	0.748	0.134	0.243
10	0.379	0.893	0.893	0.675	4.55	4.32	5.62	1.46	0.379	0.601	0.134	0.243
11	0.379	0.893	0.893	0.675	5.07	3.85	3.08	1.36	0.379	0.431	0.134	0.205
12	0.379	0.893	0.893	0.675	4.79	3.85	3.08	1.36	0.379	0.333	0.134	0.205
13	0.379	0.893	0.893	0.675	4.79	4.32	3.08	1.26	0.431	0.333	0.134	0.205
14	0.379	0.893	0.893	0.675	4.32	5.62	3.08	1.26	0.379	0.333	0.134	0.243
15	0.379	0.893	1.08	0.675	4.08	8.71	3.43	1.17	0.379	0.333	0.134	0.243
16	0.601	0.893	1.17	0.675	3.85	8.71	3.85	1.08	0.379	0.333	0.134	0.243
17	1.08	0.893	1.08	0.675	3.25	6.54	3.85	1.08	0.379	0.333	0.134	0.243
18	0.748	0.893	1.26	0.675	2.90	6.54	3.61	1.08	0.379	0.286	0.134	0.243
19	0.601	0.987	1.46	0.675	2.72	6.18	2.41	1.08	0.379	0.286	0.134	0.243
20	0.483	1.17	1.46	0.821	1.94	5.62	2.25	1.08	0.379	0.286	0.134	0.243
21	0.483	1.36	1.26	0.893	1.94	5.35	2.25	1.17	0.333	0.286	0.134	0.243
22	0.483	1.36	1.08	0.821	2.25	5.07	2.10	1.17	0.333	0.243	0.134	0.243
23	0.483	1.26	1.08	0.893	2.41	5.07	1.94	1.08	0.333	0.243	0.134	0.286
24	0.483	1.17	1.08	0.893	2.90	5.35	1.94	1.08	0.333	0.243	0.134	0.286
25	0.483	1.08	1.08	0.987	5.35	5.35	1.94	0.893	0.333	0.243	0.134	0.286
26	0.483	1.08	1.08	1.46	2.90	5.35	1.94	0.893	0.333	0.205	0.134	0.286
27	0.542	0.987	0.893	1.46	3.08	5.07	1.94	0.748	0.333	0.205	0.134	0.286
28	0.542	0.987	0.821	1.08	2.90	4.79	1.94	0.748	0.333	0.205	0.134	0.243
29	0.542	0.987	0.821	0.821	-----	4.79	1.94	0.675	0.431	0.205	0.166	0.243
30	0.483	0.987	0.821	0.893	-----	4.55	1.94	0.601	0.483	0.205	0.166	0.243
31	0.483	-----	0.821	0.893	-----	3.85	-----	0.601	-----	0.205	0.166	-----
Maks.	1.08	1.57	1.46	1.57	8.35	14.3	6.18	1.94	0.675	1.68	0.286	0.379
Min.	0.286	0.431	0.542	0.601	0.748	0.333	0.821	0.601	0.205	0.087	0.134	0.134
Ortalama	0.469	1.01	1.00	0.798	3.02	4.80	3.03	1.21	0.398	0.408	0.140	0.241
LT/SN/Km2	1.24	2.66	2.63	2.10	7.96	12.6	7.98	3.18	1.05	1.07	0.369	0.635
AKIM mm.	3.31	6.91	7.06	5.63	19.3	33.8	20.7	8.51	2.72	2.88	0.988	1.65
MİL. M3	1.26	2.62	2.68	2.14	7.32	12.9	7.86	3.23	1.03	1.09	0.375	0.625

SU YILI (2006) YILLIK TOPLAM AKIM 43.13 MİLYON M3 114 MM. 3.6 LT/SN/Km2

17. Dogu Akdeniz Havzasi

D17A041 BOZYAZI D. KARAİSALI

YERİ : **MERSİN İLİ BOZYAZI İLÇESİNE BAĞLI KARAİSALI KÖYÜNDEDİR.**
33°0'57" Doğu - 36°8'57" Kuzey

YAĞIŞ ALANI : **324,80 km2** **YAKLAŞIK KOT : 20 m**

GÖZLEM SÜRESİ : **01.10.1991 - 30.09.2006**

ORTALAMA AKIMLAR : **Gözlem süresinde NaN m3/sn. (8 Yıllık) 2006 Su yılında 4.858 m3/sn.**

ANLIK EN ÇOK VE EN AZ AKIMLAR:

2006 Su yılında anlık ençok akım	**:**	**259.**	**m3/sn**	**12.02.2006**
2006 Su yılında anlık enaz akım	**:**	**0.200**	**m3/sn**	**08.10.2005**
Gözlem süresinde anlık ençok akım	**:**	**476.**	**m3/sn**	**06.03.1996**
Gözlem süresinde anlık enaz akım	**:**	**0.000**	**m3/sn**	**01.04.1993**

Akımlar 01 Ekim 2005 'den 30 Eylül 2006' a kadar m3/sn olarak

Gün	Ekim	Kasım	Aralık	Ocak	Şubat	Mart	Nisan	Mayıs	Haziran	Temmuz	Ağustos	Eylül
01	0.250	0.290	1.00	1.60	5.20	7.39	6.56	2.10	1.10	0.740	0.420	0.250
02	0.250	1.50	0.840	1.50	4.40	7.10	6.32	2.10	1.00	0.740	0.420	0.250
03	0.250	1.00	0.840	1.35	4.00	6.81	6.32	2.00	1.00	0.740	0.420	0.250
04	0.250	4.20	0.740	1.20	3.80	6.56	6.07	2.00	1.00	0.740	0.420	0.250
05	0.250	3.60	0.660	1.10	3.60	6.32	6.07	2.00	1.00	0.740	0.420	0.250
06	0.250	2.50	0.660	1.10	5.61	6.07	5.61	1.70	1.00	0.740	0.420	0.250
07	0.250	1.90	0.560	1.10	55.8	6.07	5.61	1.70	1.00	0.740	0.420	0.250
08	0.200	1.20	0.560	1.00	93.0	5.82	5.41	1.70	1.00	0.660	0.360	0.250
09	0.200	1.10	0.560	1.00	72.1	6.56	5.20	1.70	1.00	0.660	0.360	0.250
10	0.200	0.840	0.560	1.00	63.0	6.56	5.00	1.60	0.940	0.660	0.360	0.250
11	0.200	0.500	0.500	0.940	103.	6.81	5.00	1.60	0.940	0.660	0.360	0.250
12	0.200	0.420	0.500	0.940	156.	6.81	4.80	1.60	0.940	0.660	0.360	0.250
13	0.250	0.360	0.500	0.940	114.	7.68	4.60	1.50	0.940	0.660	0.360	0.250
14	0.250	0.360	0.500	0.840	67.0	14.4	4.40	1.50	0.940	0.660	0.360	0.250
15	0.250	0.360	0.420	0.840	46.4	29.6	4.40	1.50	0.940	0.500	0.360	0.250
16	0.290	0.360	0.500	0.840	34.1	23.6	4.40	1.50	0.840	0.420	0.360	0.250
17	0.290	0.360	0.500	0.840	26.6	17.0	4.20	1.50	0.840	0.420	0.360	0.250
18	0.290	0.360	0.560	0.840	22.0	13.3	4.20	1.35	0.840	0.420	0.360	0.250
19	0.250	0.500	2.50	0.740	17.5	16.0	4.00	1.35	0.840	0.420	0.360	0.250
20	0.250	2.80	5.82	0.740	14.9	16.5	4.00	1.35	0.840	0.420	0.360	0.250
21	0.250	10.8	4.80	0.740	12.9	13.3	4.20	1.35	0.840	0.420	0.250	0.250
22	0.250	5.41	3.80	0.740	12.2	11.9	3.80	1.35	0.840	0.420	0.250	0.250
23	0.250	4.00	3.20	0.740	10.8	10.4	3.40	1.50	0.840	0.420	0.250	0.250
24	0.250	3.00	2.90	0.740	9.70	9.70	3.40	1.50	0.740	0.420	0.250	0.250
25	0.250	2.80	2.60	0.740	9.12	9.12	3.40	1.60	0.740	0.420	0.250	0.560
26	0.250	2.10	2.50	31.5	8.54	8.54	4.40	1.35	0.740	0.420	0.250	0.420
27	0.250	1.70	2.10	17.5	7.97	8.26	3.00	1.35	0.740	0.420	0.250	0.360
28	0.250	1.50	2.00	10.8	7.68	7.68	2.50	1.35	0.740	0.420	0.250	0.360
29	0.250	1.20	1.90	8.26	-----	7.39	2.30	1.35	0.740	0.420	0.250	0.360
30	0.420	1.10	1.70	6.81	-----	7.10	2.30	1.35	0.740	0.420	0.250	0.360
31	0.360	-----	1.70	5.82	-----	6.81	-----	1.20	-----	0.420	0.250	-----
Maks.	0.560	12.6	6.32	45.6	259.	33.5	6.81	2.30	1.10	0.840	0.420	1.60
Min.	0.200	0.290	0.420	0.740	3.40	5.82	2.00	1.10	0.740	0.420	0.250	0.200
Ortalama	0.255	1.94	1.56	3.38	35.4	10.2	4.50	1.57	0.888	0.549	0.335	0.281
LT/SN/Km2	0.785	5.96	4.81	10.4	109.	31.5	13.8	4.83	2.73	1.69	1.03	0.864
AKIM mm.	2.10	15.5	12.9	27.9	264.	84.4	35.9	12.9	7.09	4.53	2.76	2.24
MİL. M3	0.683	5.02	4.19	9.06	85.6	27.4	11.7	4.20	2.30	1.47	0.896	0.727

SU YILI (2006) YILLIK TOPLAM AKIM 153.25 MİLYON M3 472 MM. 15.0 LT/SN/Km2

17. Dogu Akdeniz Havzasi

D17A045 ERÇEL D. DEĞİRMENÇAY

YERİ : **MERSİN İLİ NİN 20 KM.KUZEYİNDEKİ DEĞİRMENÇAY BELDESİNDEDİR.**
34°26'25" Doğu - 36°53'28" Kuzey

YAĞIŞ ALANI : **67,00 km2** **YAKLAŞIK KOT : 460 m**

GÖZLEM SÜRESİ : **25.06.1996 - 30.09.2006**

ORTALAMA AKIMLAR : **Gözlem süresinde 1.048 m3/sn. (9 Yıllık) 2006 Su yılında 0.209 m3/sn.**

ANLIK EN ÇOK VE EN AZ AKIMLAR:

2006 Su yılında anlık ençok akım	**:**	**13.4**	**m3/sn**	**07.02.2006**
2006 Su yılında anlık enaz akım	**:**	**0.006**	**m3/sn**	**26.07.2006**
Gözlem süresinde anlık ençok akım	**:**	**88.9**	**m3/sn**	**31.03.1999**
Gözlem süresinde anlık enaz akım	**:**	**0.004**	**m3/sn**	**08.10.2001**

5. Anahtar Eğrisi (Seviyeler cm olarak)

Seviye	Akım	Seviye	Akım	Seviye	Akım	Seviye	Akım
18	0.012	57	2.6	82	8.1	160	48.7
32	0.226	62	3.4	87	9.8	210	76.2
42	0.800	67	4.4	92	12.0		
47	1.2	72	5.5	97	14.5		
52	1.8	77	6.8	110	21.6		

Akımlar 01 Ekim 2005 'den 30 Eylül 2006' a kadar m3/sn olarak

Gün	Ekim	Kasım	Aralık	Ocak	Şubat	Mart	Nisan	Mayıs	Haziran	Temmuz	Ağustos	Eylül
01	0.032	0.032	0.032	0.135	0.189	0.346	0.642	0.250	0.072	0.035	0.006	0.006
02	0.020	0.032	0.032	0.153	0.170	0.346	0.642	0.279	0.072	0.035	0.006	0.006
03	0.020	0.086	0.032	0.135	0.170	0.346	0.642	0.250	0.072	0.035	0.006	0.006
04	0.044	0.251	0.032	0.135	0.153	0.346	0.642	0.250	0.072	0.026	0.006	0.006
05	0.032	0.207	0.032	0.135	0.153	0.346	0.744	0.250	0.072	0.035	0.006	0.006
06	0.032	0.135	0.032	0.135	0.153	0.379	0.690	0.250	0.072	0.035	0.006	0.006
07	0.020	0.102	0.032	0.135	1.65	0.379	0.642	0.250	0.072	0.144	0.006	0.006
08	0.020	0.057	0.032	0.135	2.83	0.546	0.546	0.221	0.072	0.072	0.006	0.006
09	0.020	0.057	0.032	0.135	1.84	0.968	0.502	0.221	0.072	0.046	0.006	0.006
10	0.020	0.057	0.032	0.135	1.26	0.797	0.457	0.221	0.072	0.035	0.006	0.006
11	0.020	0.044	0.032	0.135	1.75	0.690	0.421	0.221	0.072	0.035	0.006	0.006
12	0.020	0.044	0.032	0.135	1.47	0.642	0.421	0.192	0.072	0.026	0.006	0.006
13	0.020	0.044	0.032	0.135	1.26	0.642	0.421	0.192	0.072	0.026	0.006	0.006
14	0.020	0.044	0.032	0.135	1.04	1.56	0.379	0.192	0.072	0.026	0.006	0.006
15	0.020	0.044	0.170	0.189	0.851	1.93	0.379	0.192	0.072	0.026	0.006	0.006
16	0.032	0.044	0.102	0.170	0.744	1.38	0.379	0.124	0.072	0.026	0.006	0.006
17	0.032	0.044	0.086	0.153	0.642	1.26	0.379	0.124	0.072	0.026	0.006	0.006
18	0.032	0.044	0.057	0.153	0.546	1.12	0.379	0.124	0.072	0.019	0.006	0.006
19	0.032	0.044	0.057	0.135	0.457	1.04	0.379	0.124	0.072	0.019	0.006	0.006
20	0.032	0.044	0.072	0.135	0.457	0.910	0.313	0.124	0.072	0.019	0.006	0.006
21	0.032	0.044	0.086	0.135	0.457	0.851	0.313	0.124	0.072	0.019	0.006	0.006
22	0.032	0.044	0.086	0.135	0.421	0.797	0.313	0.124	0.035	0.012	0.006	0.006
23	0.032	0.044	0.086	0.135	0.379	0.744	0.313	0.124	0.035	0.012	0.006	0.006
24	0.032	0.032	0.086	0.251	0.379	0.744	0.313	0.124	0.035	0.012	0.006	0.006
25	0.032	0.032	0.086	0.383	0.379	0.744	0.313	0.087	0.035	0.012	0.006	0.006
26	0.032	0.032	0.102	0.383	0.379	0.744	0.313	0.087	0.035	0.006	0.006	0.006
27	0.032	0.032	0.102	0.275	0.379	0.690	0.279	0.087	0.035	0.006	0.006	0.006
28	0.032	0.032	0.102	0.226	0.379	0.690	0.279	0.087	0.035	0.006	0.006	0.006
29	0.032	0.032	0.102	0.207	-----	0.690	0.279	0.087	0.035	0.006	0.006	0.006
30	0.032	0.032	0.102	0.207	-----	0.690	0.250	0.072	0.035	0.006	0.006	0.006
31	0.032	-----	0.102	0.189	-----	0.690	-----	0.072	-----	0.006	0.006	-----
Maks.	0.072	9.50	0.189	1.04	13.4	5.90	0.910	0.642	0.279	0.346	0.006	0.026
Min.	0.020	0.020	0.009	0.020	0.153	0.313	0.250	0.072	0.035	0.006	0.006	0.006
Ortalama	0.028	0.060	0.066	0.173	0.748	0.776	0.432	0.165	0.061	0.027	0.006	0.006
LT/SN/Km2	0.420	0.901	0.979	2.58	11.2	11.6	6.45	2.47	0.909	0.409	0.090	0.090
AKIM mm.	1.12	2.34	2.62	6.92	27.0	31.0	16.7	6.61	2.36	1.09	0.240	0.232
MİL. M3	0.075	0.157	0.176	0.464	1.81	2.08	1.12	0.443	0.158	0.073	0.016	0.016

SU YILI (2006) YILLIK TOPLAM AKIM 6.59 MİLYON M3 98 MM. 3.1 LT/SN/Km2

17. Dogu Akdeniz Havzasi

D17A046 SORGUN Ç. B.SORGUN

YERİ : **MERSİN İLİ ERDEMLİ İLÇESİ B.SORGUN BELDESİNE 5 KM. MESAFEDEKİ KÖPRÜNÜN 500 M. MANSABINDADIR**

34°9'42" Doğu - 36°50'15" Kuzey

YAĞIŞ ALANI : **268,80 km2** **YAKLAŞIK KOT : 1200 m**

GÖZLEM SÜRESİ : **01.10.1998 - 30.09.2006**

ORTALAMA AKIMLAR : **Gözlem süresinde 1.921 m3/sn. (6 Yıllık) 2006 Su yılında 0.945 m3/sn.**

ANLIK EN ÇOK VE EN AZ AKIMLAR:

2006 Su yılında anlık ençok akım	:	**9.13**	**m3/sn**	**14.03.2006**
2006 Su yılında anlık enaz akım	:	**0.032**	**m3/sn**	**07.09.2006**
Gözlem süresinde anlık ençok akım	:	**77.0**	**m3/sn**	**21.06.2003**
Gözlem süresinde anlık enaz akım	:	**0.010**	**m3/sn**	**13.07.2005**

1. Anahtar Eğrisi (Seviyeler cm olarak)

Seviye	Akım	Seviye	Akım	Seviye	Akım	Seviye	Akım
10	0.015	40	1.3	190	34.2	300	70.0
13	0.043	70	4.9	220	43.2	380	97.2
16	0.092	100	10.5	230	46.5	390	101.
19	0.162	130	18.2	240	49.8	400	105.
25	0.371	160	26.2	250	53.0	450	125.

Akımlar 01 Ekim 2005 'den 30 Eylül 2006' a kadar m3/sn olarak

Gün	Ekim	Kasım	Aralık	Ocak	Şubat	Mart	Nisan	Mayıs	Haziran	Temmuz	Ağustos	Eylül
01	0.106	0.298	0.606	0.477	0.477	2.01	3.01	1.42	0.413	0.785	0.298	0.066
02	0.106	0.353	0.606	0.477	0.542	2.01	2.87	1.42	0.413	0.606	0.298	0.044
03	0.207	0.298	0.606	0.477	0.542	2.30	2.72	1.42	0.413	0.964	0.298	0.055
04	0.298	1.31	0.606	0.477	0.542	2.58	2.72	1.31	0.353	1.31	0.207	0.055
05	0.251	0.477	0.606	0.477	0.542	2.58	2.87	1.31	0.353	0.964	0.166	0.044
06	0.251	0.413	0.606	0.477	0.785	2.58	2.58	1.19	0.251	0.875	0.166	0.044
07	0.251	0.477	0.542	0.477	2.15	3.01	2.44	1.19	0.353	1.31	0.166	0.032
08	0.251	0.606	0.542	0.477	2.72	3.18	2.44	1.19	0.353	0.785	0.166	0.055
09	0.251	0.606	0.542	0.477	2.01	3.67	2.30	1.19	0.477	0.696	0.166	0.055
10	0.251	0.606	0.542	0.477	1.65	3.51	2.15	1.19	0.477	0.606	0.166	0.055
11	0.251	0.606	0.542	0.477	3.18	3.01	2.30	1.08	0.413	0.606	0.166	0.055
12	0.251	0.606	0.477	0.477	3.01	3.34	2.15	1.08	0.413	0.606	0.166	0.066
13	0.298	0.606	0.477	0.477	2.15	3.18	2.01	0.964	0.353	0.606	0.134	0.055
14	0.298	0.606	0.477	0.477	1.65	5.65	2.01	0.964	0.353	0.542	0.134	0.055
15	0.298	0.606	0.477	0.477	1.19	6.47	1.87	0.875	0.413	0.413	0.134	0.055
16	0.298	0.606	0.542	0.477	0.875	4.84	2.44	0.875	0.413	0.353	0.134	0.044
17	0.298	0.606	0.542	0.413	0.785	4.24	1.87	1.19	0.413	0.298	0.134	0.044
18	0.298	0.696	0.606	0.477	0.785	4.24	1.87	1.08	0.353	0.298	0.134	0.066
19	0.298	0.785	1.19	0.477	0.964	3.86	1.76	0.964	0.353	0.298	0.134	0.086
20	0.298	1.31	1.42	0.477	0.964	3.51	1.65	0.964	0.353	0.298	0.086	0.066
21	0.298	1.19	0.696	0.477	1.31	3.51	1.65	0.964	0.353	0.298	0.086	0.106
22	0.298	0.785	0.606	0.477	1.65	3.86	1.65	0.875	0.353	0.298	0.086	0.251
23	0.298	0.785	0.606	0.477	1.76	4.04	1.54	0.785	0.413	0.298	0.086	0.298
24	0.298	0.696	0.606	0.696	1.76	3.86	1.76	0.696	0.353	0.298	0.086	0.298
25	0.298	0.696	0.542	1.42	2.01	4.04	1.65	0.606	0.353	0.251	0.086	0.606
26	0.298	0.696	0.542	0.964	2.15	3.86	1.54	0.606	0.353	0.251	0.086	0.542
27	0.298	0.606	0.542	0.696	1.87	3.51	1.54	0.542	0.353	0.251	0.066	0.477
28	0.298	0.606	0.542	0.606	1.76	3.51	1.54	0.477	0.477	0.251	0.066	0.413
29	0.298	0.606	0.477	0.542	-----	3.18	1.54	0.413	1.42	0.298	0.066	0.477
30	0.298	0.606	0.477	0.542	-----	3.01	1.42	0.477	0.964	0.298	0.066	0.413
31	0.298	-----	0.477	0.477	-----	3.01	-----	0.413	-----	0.298	0.066	-----
Maks.	0.964	5.45	3.34	1.87	4.43	9.13	3.18	1.54	1.87	1.31	0.353	0.964
Min.	0.106	0.298	0.298	0.207	0.477	1.76	1.42	0.353	0.251	0.166	0.055	0.032
Ortalama	0.271	0.658	0.602	0.544	1.49	3.52	2.06	0.959	0.436	0.526	0.139	0.166
LT/SN/Km2	1.01	2.45	2.24	2.02	5.55	13.1	7.67	3.57	1.62	1.96	0.516	0.617
AKIM mm.	2.70	6.35	6.00	5.42	13.4	35.1	19.9	9.55	4.20	5.24	1.38	1.60
MİL. M3	0.725	1.71	1.61	1.46	3.61	9.43	5.34	2.57	1.13	1.41	0.371	0.430

SU YILI (2006) YILLIK TOPLAM AKIM 29.80 MİLYON M3 111 MM. 3.5 LT/SN/Km2

17. Dogu Akdeniz Havzasi

D17A047 AKSIFAT D. AKSIFAT

YERİ : **İLÇEL İLİ SİLİFKE İLÇESİ SARIAYDIN KÖYÜNÜN 15 KM. KUZEYİNDEDİR.**
33°53'40" Doğu - 36°49'45" Kuzey

YAĞIŞ ALANI : **91,10 km2** **YAKLAŞIK KOT : 1500 m**

GÖZLEM SÜRESİ : **01.10.1998 - 30.09.2006**

ORTALAMA AKIMLAR : **Gözlem süresinde 1.875 m3/sn. (8 Yıllık) 2006 Su yılında 1.214 m3/sn.**

ANLIK EN ÇOK VE EN AZ AKIMLAR:

2006 Su yılında anlık ençok akım	:	**10.3**	**m3/sn**	**31.03.2006**
2006 Su yılında anlık enaz akım	:	**0.280**	**m3/sn**	**10.08.2006**
Gözlem süresinde anlık ençok akım	:	**37.3**	**m3/sn**	**05.03.2004**
Gözlem süresinde anlık enaz akım	:	**0.079**	**m3/sn**	**07.11.2000**

Akımlar 01 Ekim 2005 'den 30 Eylül 2006' a kadar m3/sn olarak

Gün	Ekim	Kasım	Aralık	Ocak	Şubat	Mart	Nisan	Mayıs	Haziran	Temmuz	Ağustos	Eylül
01	0.670	0.608	0.460	0.460	0.460	0.792	8.20	1.80	0.937	0.730	0.460	0.316
02	0.670	0.608	0.460	0.460	0.460	0.792	9.20	1.68	0.937	0.670	0.608	0.316
03	0.670	0.608	0.460	0.460	0.513	0.854	8.20	1.68	0.937	0.670	0.460	0.316
04	0.670	0.730	0.460	0.513	0.513	0.937	7.70	1.56	0.937	0.670	0.316	0.316
05	0.670	0.670	0.460	0.566	0.513	1.47	5.92	1.47	0.937	0.730	0.316	0.316
06	0.608	0.670	0.460	0.566	0.566	1.68	6.12	1.37	0.937	0.730	0.316	0.316
07	0.608	0.670	0.460	0.566	0.608	2.51	6.31	1.56	0.937	0.730	0.316	0.316
08	0.608	0.670	0.460	0.566	0.566	3.53	6.51	1.47	0.937	0.670	0.384	0.316
09	0.608	0.608	0.460	0.566	0.566	2.99	5.92	1.28	0.937	0.608	0.513	0.280
10	0.566	0.566	0.460	0.566	0.566	2.28	7.45	1.28	0.937	0.566	0.316	0.280
11	0.566	0.566	0.460	0.566	0.670	1.80	6.31	1.28	0.854	0.460	0.316	0.348
12	0.566	0.566	0.460	0.566	0.730	1.56	5.92	1.18	0.854	0.418	0.418	0.418
13	0.566	0.513	0.460	0.513	0.730	1.68	5.53	1.18	0.854	0.460	0.316	0.316
14	0.608	0.513	0.460	0.513	0.670	2.51	4.95	1.18	0.854	0.608	0.348	0.316
15	0.608	0.566	0.460	0.513	0.566	2.63	4.95	1.18	0.854	0.460	0.316	0.316
16	0.608	0.566	0.460	0.513	0.566	2.40	6.51	1.10	0.854	0.608	0.316	0.316
17	0.608	0.566	0.460	0.513	0.418	2.16	6.12	1.28	0.854	0.460	0.348	0.316
18	0.608	0.566	0.460	0.513	0.460	2.16	4.60	1.18	0.854	0.513	0.348	0.316
19	0.608	0.566	0.460	0.513	0.513	2.28	3.99	1.18	0.854	0.460	0.384	0.280
20	0.608	0.566	0.513	0.513	0.513	2.40	3.84	1.18	0.854	0.460	0.460	0.384
21	0.608	0.513	0.670	0.513	0.513	2.40	3.53	1.18	0.854	0.460	0.418	0.384
22	0.608	0.513	0.670	0.513	0.608	2.99	3.23	1.10	0.854	0.460	0.316	0.348
23	0.608	0.513	0.608	0.566	0.670	4.60	3.11	1.10	0.792	0.460	0.384	0.384
24	0.608	0.513	0.608	0.566	0.730	6.51	2.87	1.10	0.792	0.460	0.348	0.384
25	0.608	0.513	0.608	0.670	0.730	6.70	2.75	1.02	0.792	0.460	0.460	0.384
26	0.608	0.460	0.608	0.566	0.730	6.31	2.40	1.02	0.792	0.460	0.348	0.384
27	0.608	0.460	0.513	0.460	0.792	6.31	2.16	1.02	0.730	0.460	0.316	0.348
28	0.608	0.460	0.460	0.460	0.792	7.20	1.92	1.02	0.730	0.460	0.316	0.348
29	0.608	0.460	0.460	0.460	-----	7.20	1.92	1.02	0.730	0.460	0.316	0.348
30	0.608	0.460	0.460	0.460	-----	7.45	1.92	1.02	0.730	0.460	0.316	0.348
31	0.608	-----	0.460	0.460	-----	9.20	-----	0.937	-----	0.460	0.316	-----
Maks.	0.792	0.854	0.792	1.18	0.792	10.3	9.74	1.92	1.02	0.792	0.670	0.566
Min.	0.384	0.460	0.460	0.384	0.348	0.792	1.92	0.854	0.670	0.384	0.280	0.280
Ortalama	0.613	0.561	0.496	0.523	0.598	3.43	5.00	1.25	0.857	0.540	0.369	0.336
LT/SN/Km2	6.72	6.16	5.45	5.74	6.56	37.6	54.9	13.7	9.41	5.93	4.05	3.69
AKIM mm.	18.0	16.0	14.6	15.4	15.9	101.	142.	36.6	24.4	15.9	10.8	9.55
MİL. M3	1.64	1.45	1.33	1.40	1.45	9.18	13.0	3.34	2.22	1.45	0.987	0.870

SU YILI (2006) YILLIK TOPLAM AKIM 38.32 MİLYON M3 421 MM. 13.3 LT/SN/Km2

17. Dogu Akdeniz Havzasi

D17A049 LAMAS Ç. LİMONLU

YERİ : **MERSİN İLİ SİLİFKE İLÇESİ LİMONLU BELDESİ 1 KM. KUZEYİNDEDKİ MESİRE YERİNDEDİR. 34°13'34" Doğu - 36°34'33" Kuzey**

YAĞIŞ ALANI : **1356,00 km2** **YAKLAŞIK KOT : 10 m**

GÖZLEM SÜRESİ : **01.10.1999 - 30.09.2006**

ORTALAMA AKIMLAR : **Gözlem süresinde 3.210 m3/sn. (6 Yıllık) 2006 Su yılında 1.410 m3/sn.**

ANLIK EN ÇOK VE EN AZ AKIMLAR:

2006 Su yılında anlık ençok akım	:	**11.1**	**m3/sn**	**31.03.2006**
2006 Su yılında anlık enaz akım	:	**0.221**	**m3/sn**	**16.08.2006**
Gözlem süresinde anlık ençok akım	:	**89.1**	**m3/sn**	**06.03.2004**
Gözlem süresinde anlık enaz akım	:	**0.221**	**m3/sn**	**16.08.2006**

Akımlar 01 Ekim 2005 'den 30 Eylül 2006' a kadar m3/sn olarak

Gün	Ekim	Kasım	Aralık	Ocak	Şubat	Mart	Nisan	Mayıs	Haziran	Temmuz	Ağustos	Eylül
01	0.556	0.909	0.983	0.909	1.28	1.36	8.83	2.35	0.419	0.331	0.309	0.265
02	0.556	0.834	0.909	1.06	1.21	1.28	9.74	2.35	0.397	0.331	0.309	0.265
03	0.556	0.834	1.06	1.06	1.21	1.28	9.74	2.35	0.397	0.331	0.309	0.265
04	0.556	1.06	1.06	0.983	1.13	1.36	8.83	2.35	0.419	0.331	0.309	0.265
05	0.556	1.06	1.06	0.983	1.13	1.36	7.52	2.25	0.397	0.331	0.309	0.265
06	0.556	1.13	0.834	0.983	1.21	1.43	6.38	2.25	0.397	0.331	0.287	0.265
07	0.556	1.13	0.794	0.983	1.28	1.51	6.75	2.25	0.375	0.331	0.287	0.265
08	0.556	1.06	0.834	1.06	1.77	2.16	6.93	2.25	0.375	0.331	0.309	0.265
09	0.556	1.06	0.909	1.06	1.87	3.13	6.38	1.96	0.375	0.331	0.287	0.265
10	0.556	1.06	0.794	1.06	1.51	2.66	7.12	1.77	0.375	0.309	0.287	0.265
11	0.556	1.13	0.834	1.06	1.58	2.35	6.75	1.77	0.375	0.309	0.287	0.265
12	0.636	1.28	0.834	1.06	1.68	2.16	6.20	1.77	0.375	0.309	0.287	0.265
13	0.556	1.28	0.834	0.983	1.77	2.06	5.83	1.43	0.375	0.309	0.265	0.287
14	0.556	1.21	0.834	0.983	1.77	2.06	5.46	1.43	0.375	0.309	0.309	0.287
15	0.556	1.06	0.909	0.983	1.77	2.77	5.11	1.36	0.375	0.309	0.287	0.309
16	0.556	0.983	0.983	0.909	1.77	2.77	6.20	1.28	0.375	0.331	0.265	0.287
17	0.596	0.909	0.909	0.909	1.77	2.66	6.75	1.21	0.375	0.309	0.265	0.287
18	0.715	0.909	0.983	0.909	1.68	2.44	5.46	1.21	0.375	0.309	0.265	0.287
19	0.909	1.06	1.06	0.983	1.36	2.44	4.59	1.06	0.375	0.309	0.265	0.287
20	0.909	1.13	1.13	0.983	1.36	2.54	3.89	1.06	0.375	0.309	0.265	0.265
21	0.983	1.21	1.13	0.983	1.28	2.44	3.59	1.06	0.375	0.309	0.265	0.287
22	1.21	1.13	1.13	1.13	1.43	2.44	3.36	1.06	0.375	0.309	0.265	0.287
23	0.983	1.13	1.06	1.21	1.36	3.24	3.24	1.06	0.353	0.309	0.265	0.287
24	0.794	1.06	0.983	1.21	1.28	5.64	3.24	1.06	0.353	0.309	0.265	0.287
25	0.834	0.983	1.06	1.28	1.28	7.30	3.13	1.06	0.353	0.309	0.265	0.287
26	0.909	1.06	1.06	1.58	1.36	7.74	2.89	0.834	0.265	0.309	0.265	0.287
27	0.909	1.13	1.06	1.51	1.36	6.93	2.66	0.834	0.287	0.309	0.265	0.287
28	0.909	1.06	1.06	1.51	1.36	7.30	2.54	0.486	0.309	0.309	0.265	0.287
29	0.909	0.983	1.06	1.43	-----	7.74	2.44	0.419	0.309	0.309	0.265	0.331
30	0.909	0.909	0.909	1.36	-----	7.30	2.44	0.419	0.331	0.309	0.265	0.353
31	0.909	-----	0.909	1.28	-----	9.04	-----	0.486	-----	0.309	0.265	-----
Maks.	1.36	1.51	1.36	1.77	1.87	11.1	10.8	2.77	0.486	0.375	0.309	0.353
Min.	0.437	0.834	0.794	0.909	1.06	1.06	2.44	0.397	0.265	0.309	0.221	0.265
Ortalama	0.721	1.06	0.967	1.11	1.46	3.51	5.47	1.44	0.366	0.316	0.280	0.282
LT/SN/Km2	0.532	0.780	0.713	0.818	1.08	2.59	4.03	1.06	0.270	0.233	0.206	0.208
AKIM mm.	1.42	2.02	1.91	2.19	2.60	6.94	10.4	2.83	0.700	0.624	0.553	0.539
MİL. M3	1.93	2.74	2.59	2.97	3.53	9.41	14.2	3.84	0.949	0.847	0.750	0.731

SU YILI (2006) YILLIK TOPLAM AKIM 44.49 MİLYON M3 33 MM. 1.0 LT/SN/Km2

17. Dogu Akdeniz Havzasi

D17A050 LAMAS Ç. YENİYURT

YERİ : **MERSİN İLİ İLÇESİ YENİYURT KÖYÜNDEN AYRILAN TOPRAK YOLUN 3.KM SİNDE LAMAS ÇAYINI KESTİĞİ MEVKİDEDİR.**
34°6'29" Doğu - 36°36'58" Kuzey

YAĞIŞ ALANI : **1026,00 km2** **YAKLAŞIK KOT : 480 m**

GÖZLEM SÜRESİ : **01.04.1998 - 30.09.2006**

ORTALAMA AKIMLAR : **Gözlem süresinde 3.865 m3/sn. (8 Yıllık) 2006 Su yılında 1.857 m3/sn.**

ANLIK EN ÇOK VE EN AZ AKIMLAR:

2006 Su yılında anlık ençok akım	:	**11.2**	**m3/sn**	**31.03.2006**
2006 Su yılında anlık enaz akım	:	**0.044**	**m3/sn**	**13.08.2006**
Gözlem süresinde anlık ençok akım	:	**91.0**	**m3/sn**	**06.03.2004**
Gözlem süresinde anlık enaz akım	:	**0.044**	**m3/sn**	**13.08.2006**

Akımlar 01 Ekim 2005 'den 30 Eylül 2006' a kadar m3/sn olarak

Gün	Ekim	Kasım	Aralık	Ocak	Şubat	Mart	Nisan	Mayıs	Haziran	Temmuz	Ağustos	Eylül
01	0.779	0.974	1.17	1.36	1.46	1.88	10.6	3.13	1.46	1.07	0.779	0.156
02	0.682	0.876	1.17	1.27	1.46	2.02	10.3	2.87	1.46	1.07	0.298	0.092
03	0.779	1.07	1.17	1.27	1.46	2.02	10.0	3.13	1.36	1.17	0.393	0.779
04	0.779	1.17	1.17	1.27	1.46	2.02	9.75	3.13	1.36	1.07	0.584	1.07
05	0.779	1.27	1.17	1.27	1.46	2.17	9.16	2.87	1.17	1.07	0.393	0.298
06	0.682	1.36	1.17	1.27	1.46	2.45	7.72	2.87	1.36	1.07	0.251	0.092
07	0.584	1.36	1.17	1.27	1.88	2.45	8.01	2.73	1.36	0.974	0.440	0.124
08	0.682	1.17	1.07	1.27	2.17	3.64	8.29	2.73	1.36	1.07	0.393	0.092
09	0.779	1.46	1.07	1.27	2.17	4.42	7.44	2.73	1.36	0.974	0.187	0.124
10	0.779	1.07	0.974	1.27	1.88	3.39	8.87	2.59	1.36	0.876	0.187	0.124
11	0.682	0.876	0.974	1.27	2.02	2.87	8.29	2.45	1.36	0.779	0.251	0.251
12	0.584	0.876	0.876	1.27	2.02	2.59	7.72	2.31	1.36	0.682	0.156	0.345
13	0.584	0.974	0.876	1.27	2.17	2.59	7.44	2.17	1.36	0.682	0.044	0.393
14	0.876	0.974	0.876	1.27	2.02	2.87	7.15	2.02	1.27	0.682	0.156	0.440
15	0.876	0.974	0.974	1.17	1.74	3.90	6.87	2.02	1.27	0.779	0.156	0.393
16	0.682	1.17	0.974	1.07	1.74	3.90	7.72	2.02	1.17	0.876	0.068	0.298
17	1.17	1.17	0.974	1.07	1.74	3.64	8.29	2.17	1.17	0.682	0.187	0.219
18	1.17	1.27	1.07	1.07	1.74	3.13	7.15	2.17	1.17	0.682	0.156	0.187
19	0.876	1.27	1.17	1.17	1.60	3.13	5.73	2.31	1.17	0.584	0.156	0.156
20	0.876	1.36	1.27	1.17	1.60	3.39	5.19	2.17	1.07	0.487	0.187	0.219
21	0.974	1.36	1.27	1.17	1.60	3.64	5.19	2.02	1.07	0.487	0.156	0.584
22	1.07	1.36	1.27	1.17	1.60	3.64	4.93	1.88	0.974	0.487	0.187	0.156
23	0.779	1.36	1.46	1.27	1.60	5.19	4.68	1.88	1.07	0.779	0.298	0.345
24	0.682	1.27	1.46	1.36	1.60	7.44	4.68	1.74	0.974	0.876	0.298	0.584
25	0.779	1.27	1.36	1.74	1.60	8.58	4.42	1.88	0.876	0.682	0.298	0.393
26	0.682	1.27	1.36	1.74	2.02	8.58	4.16	1.74	0.779	0.487	0.251	0.345
27	0.584	1.27	1.36	1.60	1.88	8.29	3.64	1.60	0.779	0.219	0.440	0.345
28	0.584	1.27	1.36	1.46	1.88	8.58	3.39	1.60	0.876	0.779	0.298	0.440
29	0.682	1.17	1.36	1.46	-----	8.87	3.13	1.60	0.974	0.682	0.219	0.440
30	0.974	1.17	1.36	1.46	-----	9.75	3.13	1.46	1.07	0.876	0.156	0.487
31	0.974	-----	1.27	1.46	-----	10.6	-----	1.46	-----	0.779	0.124	-----
Maks.	1.36	1.46	1.74	2.02	2.31	11.2	11.2	4.16	2.59	1.60	0.876	1.27
Min.	0.345	0.682	0.682	0.974	1.36	1.88	2.59	1.17	0.584	0.092	0.044	0.044
Ortalama	0.789	1.18	1.17	1.31	1.75	4.57	6.77	2.24	1.18	0.789	0.263	0.332
LT/SN/Km2	0.769	1.15	1.14	1.27	1.71	4.45	6.60	2.18	1.15	0.769	0.256	0.324
AKIM mm.	2.06	2.99	3.05	3.41	4.13	11.9	17.1	5.85	2.98	2.06	0.686	0.840
MİL. M3	2.11	3.06	3.13	3.50	4.24	12.2	17.5	6.00	3.06	2.11	0.704	0.861

SU YILI (2006) YILLIK TOPLAM AKIM 58.47 MİLYON M3 57 MM. 1.8 LT/SN/Km2

17. Dogu Akdeniz Havzasi

D17A051 PİRİNÇ S. GENÇALİ

YERİ : **MERSİN İLİ MUT İLÇESİ GENÇALİ KÖYÜNÜN 1.5 KM KUZEYİNDEKİ REGÜLATÖRÜN 10 M MENBAAINDADIR 33°26'25" Doğu - 36°42'33" Kuzey**

YAĞIŞ ALANI : **502,00 km2** **YAKLAŞIK KOT : 180 m**

GÖZLEM SÜRESİ : **21.06.2001 - 30.09.2006**

ORTALAMA AKIMLAR : **Gözlem süresinde 0.972 m3/sn. (4 Yıllık) 2006 Su yılında 1.044 m3/sn.**

ANLIK EN ÇOK VE EN AZ AKIMLAR:

2006 Su yılında anlık ençok akım	:	**32.3**	**m3/sn**	**02.04.2006**
2006 Su yılında anlık enaz akım	:	**0.000**	**m3/sn**	**24.10.2005**
Gözlem süresinde anlık ençok akım	:	**137.**	**m3/sn**	**05.03.2004**
Gözlem süresinde anlık enaz akım	:	**0.000**	**m3/sn**	**23.05.2005**

Akımlar 01 Ekim 2005 'den 30 Eylül 2006' a kadar m3/sn olarak

Gün	Ekim	Kasım	Aralık	Ocak	Şubat	Mart	Nisan	Mayıs	Haziran	Temmuz	Ağustos	Eylül
01	0.243	0.112	0.035	0.243	0.508	1.85	5.09	0.898	0.163	0.216	0.129	0.064
02	0.243	0.129	0.129	0.216	0.508	2.23	16.4	1.27	0.146	0.163	0.129	0.064
03	0.243	0.163	0.112	0.190	0.579	2.61	7.97	1.85	0.129	0.163	0.129	0.064
04	0.269	0.898	0.095	0.190	0.508	2.99	6.05	1.02	0.112	0.163	0.146	0.078
05	0.367	0.269	0.112	0.163	0.508	2.61	4.61	0.898	0.112	0.146	0.112	0.078
06	0.243	0.243	0.078	0.190	1.85	2.42	3.94	0.898	0.112	0.163	0.078	0.078
07	0.243	0.269	0.035	0.163	7.49	2.80	3.56	0.898	0.095	0.163	0.129	0.078
08	0.296	0.243	0.078	0.269	10.4	3.18	3.37	0.774	0.078	0.163	0.112	0.078
09	0.243	0.190	0.129	0.243	3.94	3.37	2.99	0.650	0.078	0.146	0.078	0.078
10	0.243	0.163	0.112	0.190	2.61	2.61	2.99	0.579	0.095	0.146	0.095	0.078
11	0.269	0.163	0.129	0.243	11.9	2.23	2.80	0.650	0.112	0.129	0.129	0.078
12	0.296	0.163	0.190	0.243	11.4	2.23	2.61	0.650	0.112	0.129	0.129	0.095
13	0.163	0.112	0.163	0.243	5.57	2.61	2.42	0.650	0.129	0.146	0.129	0.112
14	0.129	0.078	0.163	0.216	2.80	10.4	2.04	1.27	0.129	0.146	0.129	0.112
15	0.035	0.049	0.095	0.216	1.85	13.4	2.23	1.27	0.129	0.129	0.112	0.112
16	0.027	0.078	0.049	0.243	1.15	8.93	4.13	1.27	0.112	0.146	0.064	0.129
17	0.078	0.078	0.095	0.216	1.02	7.01	2.80	1.27	0.078	0.129	0.078	0.129
18	0.190	0.095	0.095	0.216	1.02	5.57	2.42	1.27	0.078	0.129	0.129	0.146
19	0.078	0.095	0.650	0.243	0.898	4.13	2.23	0.774	0.095	0.129	0.129	0.129
20	0.064	0.243	1.46	0.269	1.15	3.75	1.85	0.438	0.078	0.129	0.112	0.129
21	0.129	0.438	0.508	0.243	1.02	3.37	1.65	0.243	0.064	0.129	0.078	0.129
22	0.078	0.190	0.508	0.269	1.15	3.56	1.46	0.367	0.049	0.095	0.095	0.129
23	0.010	0.129	0.296	0.438	1.46	3.94	1.85	0.367	0.049	0.095	0.112	0.146
24	KURU	0.129	0.269	0.508	1.85	5.09	2.23	0.367	0.064	0.112	0.112	0.146
25	KURU	0.129	0.296	2.04	2.04	5.09	2.80	0.367	0.367	0.078	0.129	0.146
26	KURU	0.112	0.216	1.65	2.42	4.13	2.23	0.367	0.269	0.049	0.095	0.146
27	0.010	0.095	0.269	0.898	2.42	3.94	1.85	0.296	0.216	0.049	0.064	0.190
28	0.049	0.129	0.269	0.650	1.85	3.94	1.65	0.269	0.243	0.064	0.035	0.163
29	0.049	0.112	0.367	0.367	-----	3.75	1.65	0.243	0.243	0.064	0.035	0.146
30	0.095	0.112	0.367	0.438	-----	3.56	1.15	0.216	0.243	0.078	0.064	0.146
31	0.078	-----	0.367	0.438	-----	3.94	-----	0.163	-----	0.078	0.064	-----
Maks.	0.650	3.75	2.23	3.75	22.5	17.4	32.3	3.94	1.65	0.243	0.163	0.296
Min.	KURU	0.035	0.035	0.018	0.146	0.243	0.163	0.035	0.049	0.049	0.027	0.064
Ortalama	0.144	0.180	0.250	0.398	2.92	4.23	3.37	0.726	0.133	0.125	0.102	0.113
LT/SN/Km2	0.287	0.359	0.497	0.793	5.82	8.43	6.71	1.45	0.264	0.248	0.203	0.225
AKIM mm.	0.768	0.931	1.33	2.12	14.1	22.6	17.4	3.87	0.685	0.665	0.544	0.584
MİL. M3	0.385	0.467	0.668	1.07	7.07	11.3	8.73	1.95	0.344	0.334	0.273	0.293

SU YILI (2006) YILLIK TOPLAM AKIM 32.88 MİLYON M3 66 MM. 2.1 LT/SN/Km2

17. Dogu Akdeniz Havzasi

D17A053 GÖKSU N. KARGICAK

YERİ : **SİLİFKE-MUT KARAYOLUNUN KARGICAK MEVKİİNDE SOLA AYRILAN KÖY YOLUNUN 1.KM SİNDEKİ KÖPRÜDEDİR.**
33°38'44" Doğu - 36°26'31" Kuzey

YAĞIŞ ALANI : **9765,00 km2** **YAKLAŞIK KOT : 58 m**

GÖZLEM SÜRESİ : **01.10.2002 - 30.09.2006**

ORTALAMA AKIMLAR : **Gözlem süresinde 80.883 m3/sn. (4 Yıllık) 2006 Su yılında 67.792 m3/sn.**

ANLIK EN ÇOK VE EN AZ AKIMLAR:

2006 Su yılında anlık ençok akım	**:**	**319.**	**m3/sn**	**18.04.2006**
2006 Su yılında anlık enaz akım	**:**	**15.6**	**m3/sn**	**18.09.2006**
Gözlem süresinde anlık ençok akım	**:**	**2785**	**m3/sn**	**06.03.2004**
Gözlem süresinde anlık enaz akım	**:**	**13.1**	**m3/sn**	**23.07.2004**

Akımlar 01 Ekim 2005 'den 30 Eylül 2006' a kadar m3/sn olarak

Gün	Ekim	Kasım	Aralık	Ocak	Şubat	Mart	Nisan	Mayıs	Haziran	Temmuz	Ağustos	Eylül
01	35.4	38.9	48.4	44.6	41.0	161.	224.	69.2	42.7	34.4	36.0	27.7
02	32.0	38.9	53.9	37.1	36.7	150.	225.	78.4	40.8	32.8	33.7	25.8
03	30.4	36.3	52.4	38.9	34.5	146.	226.	77.7	40.3	30.8	35.0	25.4
04	34.9	43.1	52.4	37.6	34.9	146.	218.	81.6	34.4	33.1	33.4	26.8
05	34.9	37.6	44.1	38.5	30.4	137.	216.	69.2	32.8	33.4	36.3	28.4
06	34.5	36.3	45.2	42.5	34.9	148.	209.	52.6	36.3	34.0	33.1	27.4
07	34.5	37.1	51.5	41.0	54.4	168.	189.	46.3	37.6	33.4	34.4	27.4
08	34.5	38.0	51.0	35.8	128.	174.	183.	54.2	32.8	37.0	35.7	27.4
09	34.1	42.0	51.0	30.8	188.	176.	200.	56.8	35.3	29.8	35.3	28.1
10	34.1	38.0	50.0	30.8	134.	169.	196.	76.1	35.0	30.1	35.7	22.5
11	34.5	37.1	47.9	34.9	145.	189.	199.	49.4	30.8	32.8	36.3	19.0
12	34.5	36.7	44.6	35.8	195.	142.	194.	47.6	31.5	33.7	30.4	18.8
13	34.9	41.5	49.0	35.8	206.	135.	196.	46.7	34.4	34.0	29.8	19.0
14	34.5	36.7	50.5	35.8	189.	138.	195.	45.8	30.8	34.7	32.1	42.7
15	34.5	46.3	50.5	35.4	137.	202.	205.	45.0	31.1	31.5	34.4	21.1
16	34.9	45.2	50.5	38.0	114.	179.	215.	43.2	30.8	32.1	37.0	19.3
17	32.5	46.3	50.0	44.6	126.	158.	253.	41.2	31.1	33.7	38.0	18.8
18	35.4	46.3	51.0	42.0	124.	173.	293.	38.0	29.8	34.4	35.0	16.7
19	35.4	45.7	59.1	40.5	114.	167.	256.	41.7	28.4	35.3	32.8	16.7
20	36.3	43.1	70.7	54.4	123.	169.	228.	42.2	34.7	34.4	31.1	16.7
21	36.7	47.3	85.1	51.0	118.	126.	164.	37.6	31.1	35.3	32.4	16.7
22	37.6	90.5	73.4	56.2	106.	134.	146.	38.0	32.8	34.0	42.2	16.7
23	36.7	69.3	85.1	53.9	107.	147.	136.	40.3	32.8	31.1	36.0	21.1
24	34.1	63.1	68.0	74.8	118.	162.	136.	38.8	32.1	31.1	37.0	21.5
25	36.3	51.5	68.7	65.9	121.	227.	104.	38.8	30.1	34.4	36.0	20.1
26	38.0	43.1	61.7	74.8	115.	231.	91.7	37.6	33.1	35.0	34.0	19.6
27	38.9	40.5	50.0	68.0	128.	222.	74.5	35.3	32.4	37.0	28.7	19.0
28	37.1	41.5	49.5	72.7	161.	221.	65.3	31.8	33.7	35.7	28.7	19.0
29	36.7	47.3	51.0	56.2	-----	219.	64.4	34.7	34.4	34.4	30.4	19.0
30	28.8	43.1	49.5	47.9	-----	218.	63.0	44.5	34.0	28.4	28.1	19.0
31	33.7	-----	47.9	45.2	-----	219.	-----	44.5	-----	30.1	26.8	-----
Maks.	52.9	110.	109.	160.	213.	245.	319.	122.	60.4	90.9	77.7	61.5
Min.	18.9	23.2	31.6	24.9	27.9	98.5	43.2	30.1	26.4	25.4	25.4	15.6
Ortalama	34.9	44.9	55.3	46.5	113.	173.	179.	49.2	33.6	33.3	33.7	22.2
LT/SN/Km2	3.57	4.60	5.66	4.76	11.6	17.7	18.3	5.04	3.44	3.41	3.45	2.28
AKIM mm.	9.57	11.9	15.2	12.8	28.0	47.4	47.5	13.5	8.92	9.13	9.25	5.91
MİL. M3	93.4	116.	148.	125.	273.	462.	464.	132.	87.1	89.2	90.4	57.7

SU YILI (2006) YILLIK TOPLAM AKIM 2137.80 MİLYON M3 219 MM. 6.9 LT/SN/Km2

17. Dogu Akdeniz Havzasi

D17A054 CEHENNEM D. SEBİL

YERİ : **MERSİN İLİ ÇAMLIYAYLA İLÇESİ SEBİL-CEHENNEM DERE YOLUNUN 14KM. SİNDEKİ KÖPRÜNÜN 100 M MENBASINDADIR.**
34°31'52" Doğu - 37°7'15" Kuzey

YAĞIŞ ALANI : **340,00 km2** **YAKLAŞIK KOT : 615 m**

GÖZLEM SÜRESİ : **01.10.2004 - 30.09.2006**

ORTALAMA AKIMLAR : **Gözlem süresinde NaN m3/sn. (2 Yıllık) 2006 Su yılında 6.307 m3/sn.**

ANLIK EN ÇOK VE EN AZ AKIMLAR:

2006 Su yılında anlık ençok akım	**:**	**35.8**	**m3/sn**	**16.04.2006**
2006 Su yılında anlık enaz akım	**:**	**0.848**	**m3/sn**	**29.09.2006**
Gözlem süresinde anlık ençok akım	**:**	**60.6**	**m3/sn**	**22.04.2005**
Gözlem süresinde anlık enaz akım	**:**	**0.848**	**m3/sn**	**29.09.2006**

2. Anahtar Eğrisi (Seviyeler cm olarak)

Seviye	Akım	Seviye	Akım	Seviye	Akım	Seviye	Akım
18	0.428	70	13.2	170	56.9	260	100.
22	0.748	90	20.9	190	66.4	270	106.
26	1.2	110	29.4	210	75.0	280	112.
30	1.7	130	38.5	230	85.1	290	117.
50	6.1	150	47.7	250	94.7	300	122.

Akımlar 01 Ekim 2005 'den 30 Eylül 2006' a kadar m3/sn olarak

Gün	Ekim	Kasım	Aralık	Ocak	Şubat	Mart	Nisan	Mayıs	Haziran	Temmuz	Ağustos	Eylül
01	1.39	1.68	4.06	2.60	1.68	5.33	14.3	15.1	12.8	5.66	2.60	1.83
02	1.39	1.68	4.06	2.41	1.68	6.31	18.0	15.5	11.7	5.08	2.60	1.68
03	1.39	1.68	4.82	2.79	1.68	6.96	16.3	15.9	11.3	5.08	2.60	1.68
04	1.39	6.96	5.08	2.60	1.83	7.29	16.3	13.6	11.0	5.98	2.41	1.68
05	1.39	5.08	4.57	2.60	2.02	6.96	14.0	12.0	11.0	6.96	2.41	1.68
06	1.39	4.31	4.06	2.60	2.21	6.63	13.2	12.4	10.6	7.61	2.60	1.68
07	1.39	4.57	3.55	2.60	5.66	6.96	14.3	14.0	10.3	7.29	2.60	1.68
08	1.39	3.55	3.30	2.60	7.61	7.29	18.4	14.3	9.27	6.31	2.60	1.68
09	1.39	3.04	3.04	2.41	7.29	8.26	18.8	14.3	8.59	5.08	2.60	1.68
10	1.39	2.79	2.79	2.41	5.98	7.29	24.3	12.8	7.94	4.82	2.41	1.68
11	1.39	2.79	2.79	2.41	5.98	6.96	24.3	13.6	7.29	4.57	2.41	1.54
12	1.39	2.60	2.79	2.41	6.31	6.63	24.7	15.9	6.96	4.31	2.41	1.54
13	1.39	2.60	2.60	2.41	5.33	6.63	27.7	17.6	6.96	4.06	2.21	1.54
14	1.39	2.21	2.60	2.41	4.82	12.0	26.5	15.9	6.96	4.06	2.21	1.54
15	1.39	2.02	2.79	2.41	4.31	13.6	24.7	15.5	6.63	4.06	2.21	1.54
16	1.39	2.02	2.79	2.02	3.81	10.6	30.8	16.3	6.31	3.81	2.02	1.54
17	1.83	2.02	2.79	1.68	3.55	9.61	30.8	14.3	5.98	3.55	2.02	1.54
18	1.68	3.04	3.30	1.68	3.30	9.61	24.3	12.0	5.66	3.55	2.02	1.54
19	1.68	5.08	7.29	1.68	3.30	9.61	26.5	12.4	5.33	3.55	2.02	1.54
20	1.68	7.94	6.31	1.68	4.06	8.93	24.3	12.8	5.33	3.30	2.02	1.54
21	1.68	8.59	4.82	1.68	3.81	8.59	22.6	14.3	5.08	3.30	2.02	1.39
22	1.68	5.33	4.06	1.68	5.08	9.95	21.8	15.9	5.08	3.30	2.02	1.39
23	1.68	4.31	4.06	1.68	5.98	12.8	19.7	18.4	4.82	3.30	2.02	1.39
24	1.68	3.55	3.81	2.02	6.31	14.7	18.4	18.8	4.82	3.04	2.02	1.39
25	1.68	3.55	3.30	3.04	6.63	14.7	16.3	17.6	4.57	3.04	2.02	1.39
26	1.68	3.81	3.04	3.30	6.96	13.6	14.0	16.7	4.57	3.04	1.83	1.39
27	1.68	4.82	3.04	2.79	6.63	11.7	12.8	16.7	5.66	2.79	1.83	1.39
28	1.68	4.82	2.79	2.02	5.66	11.7	12.4	15.9	6.31	2.79	1.83	1.39
29	1.68	4.57	2.79	1.83	-----	12.0	12.4	15.1	6.31	2.79	1.83	1.39
30	1.68	4.31	2.60	1.68	-----	12.8	12.8	14.3	6.31	2.79	1.83	1.39
31	1.68	-----	2.60	1.68	-----	14.7	-----	14.0	-----	2.79	1.83	-----
Maks.	2.21	13.6	8.93	4.06	7.94	21.8	35.8	22.2	14.7	16.3	2.79	2.02
Min.	1.39	1.68	2.41	1.68	1.68	5.33	12.0	11.7	4.57	2.79	1.54	0.848
Ortalama	1.54	3.84	3.62	2.25	4.62	9.70	19.9	15.0	7.38	4.25	2.20	1.54
LT/SN/Km2	4.52	11.3	10.7	6.62	13.6	28.5	58.4	44.0	21.7	12.5	6.46	4.53
AKIM mm.	12.1	29.3	28.5	17.7	32.9	76.4	151.	118.	56.3	33.5	17.3	11.8
MİL. M3	4.11	9.96	9.70	6.03	11.2	26.0	51.5	40.1	19.1	11.4	5.88	4.00

SU YILI (2006) YILLIK TOPLAM AKIM 198.98 MİLYON M3 585 MM. 18.6 LT/SN/Km2

18

SEYHAN HAVZASI

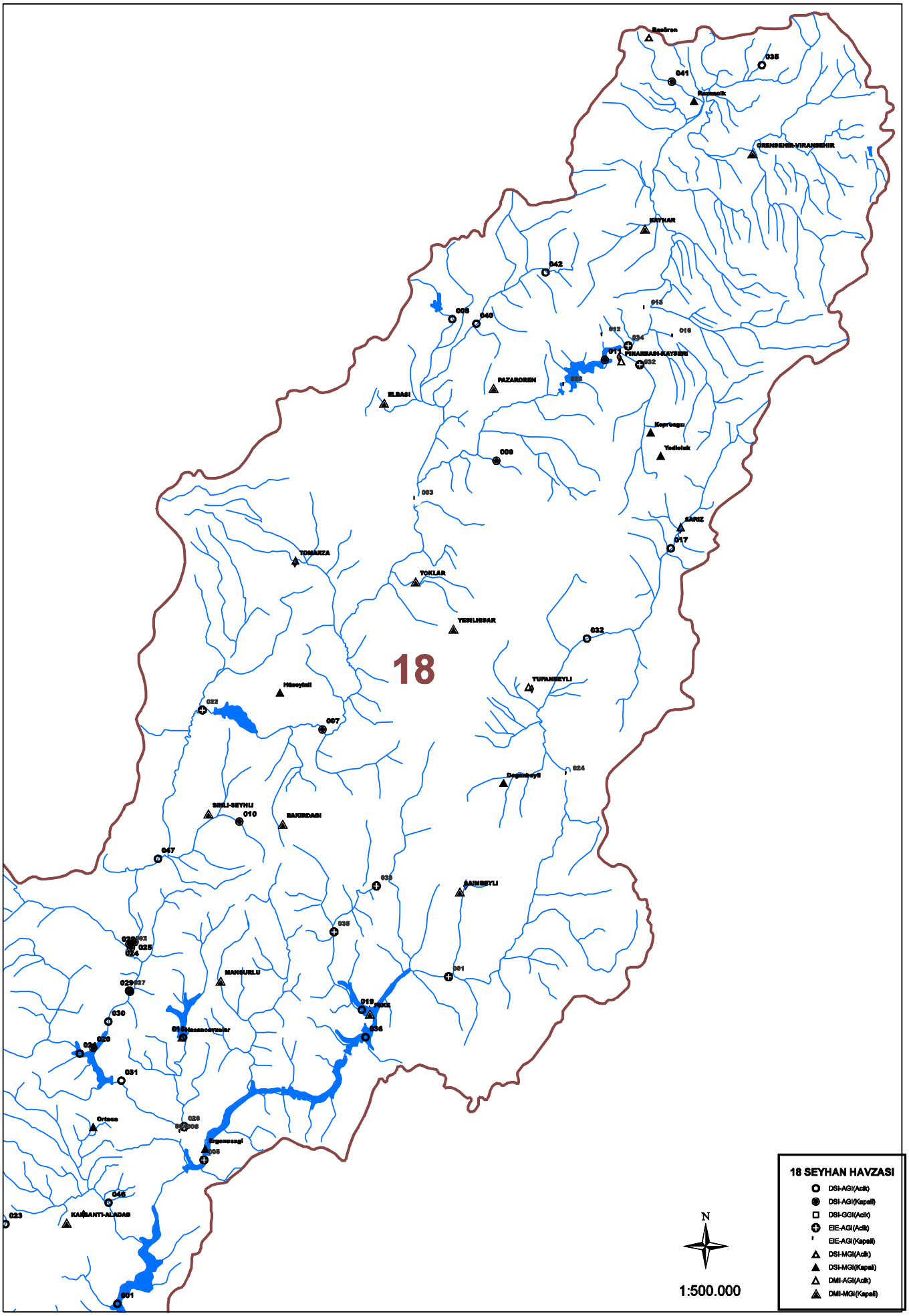
18
18 SEYHAN HAVZASI
DSI-AGI(Acik)
DSI-AGI(Kapali)
DSI-GGI(Acik)
EIE-AGI(Acik)
EIE-AGI(Kapali)
DSI-MGI(Acik)
DSI-MGI(Kapali)
DMI-AGI(Acik)
DMI-MGI(Kapali)
N
1:500.000
Bacören
Kozanalik
ÖRENSEHIR-VIRANSEHIR
KAYNAR
PINARBASI-KAYSERI
PAZAROREN
ELBASI
Kopruoguz
Yedioluk
SARIZ
TOMARZA
TOKLAR
YENILIGSAR
TUFANBEYLI
Hisseyinli
Degirmeyli
SIRLI-SEYHLI
BAKIRDAGI
SAIMBEYLI
MANSURLU
PINE
Orisna
Irgenusagi
KAHRANTI-ALADAG

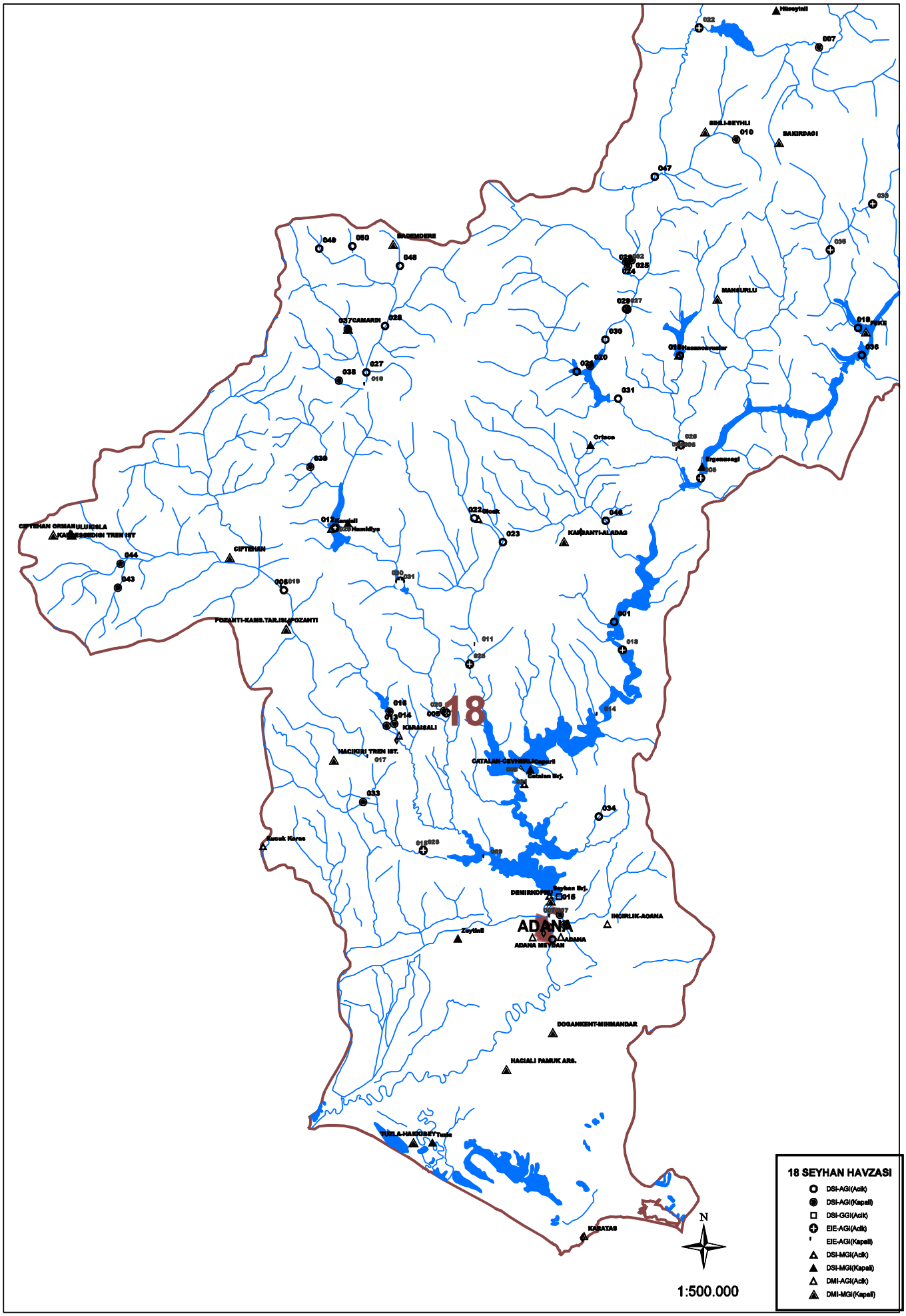
18
ADANA
SIRLI-SEYHLI
BAKIRDAGI
BADEMDERE
CAMARDI
MANSURLU
Ortaca
Ergenesagi
CIPTEHAN ORMANULUKISLA
CIPTEHAN
POZANTI-KAMS.TAR.ISL.POZANTI
KARAISALI
HACIKIRI TREN IST.
CATALAN-DEVREKLI
DEMIRKOPRU
INCIRLIK-ADANA
ADANA MEYDAN
Zeytinli
DOGANKENT-MIHMANDAR
HACIALI PAMUK ARS.
KARATAS
N
1:500.000
18 SEYHAN HAVZASI
DSI-AGI(Acik)
DSI-AGI(Kapali)
DSI-GGI(Acik)
EIE-AGI(Acik)
EIE-AGI(Kapali)
DSI-MGI(Acik)
DSI-MGI(Kapali)
DMI-AGI(Acik)
DMI-MGI(Kapali)

18. Seyhan Havzasi

D18A001 SEYHAN N. EYNER

YERİ : **ADANA- ALADAĞ KARAYOLU ÜZERİNDEKİ EYNER KÖYÜNDE BULANAN SEYHAN NEHRİ KÖPRÜSÜNDEEDİR**
35°27'17" Doğu - 37°25'21" Kuzey

YAĞIŞ ALANI : **13780,00 km2** **YAKLAŞIK KOT : 200 m**

GÖZLEM SÜRESİ : **01.10.2003 - 30.09.2006**

ORTALAMA AKIMLAR : **Gözlem süresinde 111.075 m3/sn. (3 Yıllık) 2006 Su yılında 104.811 m3/sn.**

ANLIK EN ÇOK VE EN AZ AKIMLAR:

2006 Su yılında anlık ençok akım	**:**	**420.**	**m3/sn**	**09.03.2006**
2006 Su yılında anlık enaz akım	**:**	**42.1**	**m3/sn**	**10.10.2005**
Gözlem süresinde anlık ençok akım	**:**	**1600**	**m3/sn**	**19.12.1962**
Gözlem süresinde anlık enaz akım	**:**	**42.1**	**m3/sn**	**10.10.2005**

Akımlar 01 Ekim 2005 'den 30 Eylül 2006' a kadar m3/sn olarak

Gün	Ekim	Kasım	Aralık	Ocak	Şubat	Mart	Nisan	Mayıs	Haziran	Temmuz	Ağustos	Eylül
01	49.4	47.8	58.7	74.8	65.0	174.	238.	154.	84.8	84.8	58.7	57.1
02	49.4	49.4	57.1	74.8	65.0	180.	255.	145.	83.2	83.2	58.7	57.1
03	49.4	47.8	57.1	71.5	65.0	202.	268.	139.	83.2	78.2	58.7	57.1
04	50.9	79.8	58.7	69.8	68.2	249.	238.	137.	83.2	78.2	57.1	55.6
05	49.4	73.1	58.7	68.2	69.8	240.	264.	130.	81.5	84.8	57.1	55.6
06	49.4	58.7	58.7	66.6	73.1	217.	232.	133.	79.8	81.5	57.1	54.0
07	47.8	54.0	57.1	66.6	106.	215.	215.	132.	83.2	79.8	57.1	55.6
08	46.3	52.5	60.2	66.6	264.	236.	202.	130.	81.5	78.2	55.6	54.0
09	47.8	52.5	60.2	63.4	275.	383.	198.	137.	81.5	76.5	55.6	54.0
10	46.3	52.5	60.2	65.0	198.	331.	202.	135.	81.5	74.8	55.6	49.4
11	46.3	49.4	58.7	66.6	257.	268.	204.	132.	78.2	74.8	55.6	50.9
12	46.3	50.9	58.7	69.8	286.	236.	219.	128.	78.2	71.5	55.6	55.6
13	46.3	49.4	58.7	71.5	355.	225.	227.	128.	78.2	69.8	55.6	52.5
14	46.3	47.8	58.7	71.5	291.	223.	229.	132.	78.2	68.2	55.6	49.4
15	46.3	47.8	58.7	71.5	242.	244.	221.	126.	78.2	69.8	54.0	52.5
16	52.5	49.4	63.4	65.0	204.	242.	219.	124.	74.8	68.2	54.0	46.3
17	73.1	49.4	66.6	61.8	176.	234.	219.	128.	74.8	68.2	58.7	46.3
18	58.7	47.8	76.5	61.8	160.	234.	208.	122.	73.1	65.0	57.1	46.3
19	61.8	47.8	298.	66.6	147.	268.	200.	120.	71.5	65.0	58.7	46.3
20	54.0	50.9	244.	66.6	141.	242.	188.	117.	71.5	63.4	63.4	46.3
21	52.5	95.3	174.	61.8	135.	229.	186.	113.	69.8	63.4	58.7	46.3
22	50.9	109.	147.	65.0	135.	213.	184.	111.	68.2	65.0	57.1	47.8
23	50.9	79.8	117.	65.0	137.	211.	184.	109.	68.2	61.8	58.7	47.8
24	50.9	71.5	106.	66.6	139.	221.	184.	108.	66.6	63.4	57.1	49.4
25	50.9	65.0	97.0	73.1	143.	275.	190.	102.	65.0	61.8	55.6	57.1
26	50.9	61.8	88.3	97.0	149.	331.	186.	97.0	66.6	61.8	57.1	55.6
27	49.4	60.2	90.0	97.0	162.	279.	168.	95.3	66.6	61.8	57.1	55.6
28	50.9	58.7	81.5	84.8	172.	255.	160.	93.5	69.8	60.2	58.7	57.1
29	50.9	60.2	76.5	74.8	-----	244.	158.	91.8	81.5	60.2	57.1	46.3
30	49.4	60.2	76.5	68.2	-----	234.	154.	88.3	90.0	60.2	57.1	54.0
31	49.4	-----	78.2	65.0	-----	238.	-----	86.5	-----	58.7	57.1	-----
Maks.	90.0	141.	338.	120.	388.	420.	369.	162.	126.	149.	71.5	95.3
Min.	42.1	44.9	50.9	58.7	60.2	170.	149.	86.5	61.8	54.0	52.5	46.3
Ortalama	50.8	59.3	89.1	70.3	167.	244.	207.	120.	76.4	69.7	57.1	52.0
LT/SN/Km2	3.69	4.31	6.46	5.10	12.1	17.7	15.0	8.72	5.55	5.06	4.15	3.77
AKIM mm.	9.87	11.2	17.3	13.7	29.3	47.5	38.9	23.4	14.4	13.6	11.1	9.77
MİL. M3	136.	154.	239.	188.	404.	654.	536.	322.	198.	187.	153.	135.

SU YILI (2006) YILLIK TOPLAM AKIM 3306.00 MİLYON M3 240 MM. 7.6 LT/SN/Km2

18. Seyhan Havzasi

D18A006 ÇAKIT S. ŞEKERPINARI

YERİ : **ADANA-ANKARA KARAYOLUNUN 118 KM. SİNDEKİ ŞEKERPINARI MEVKİİNDEKİ TARİHİ KÖPRÜDEDİR**
34°51'43" Doğu - 37°28'15" Kuzey

YAĞIŞ ALANI : **1234,00 km2** **YAKLAŞIK KOT : 800 m**

GÖZLEM SÜRESİ : **01.10.1992 - 30.09.2006**

ORTALAMA AKIMLAR : **Gözlem süresinde 8.668 m3/sn. (13 Yıllık) 2006 Su yılında 4.448 m3/sn.**

ANLIK EN ÇOK VE EN AZ AKIMLAR:

2006 Su yılında anlık ençok akım	**:**	**43.2**	**m3/sn**	**04.11.2005**
2006 Su yılında anlık enaz akım	**:**	**0.640**	**m3/sn**	**10.10.2005**
Gözlem süresinde anlık ençok akım	**:**	**145.**	**m3/sn**	**05.12.1996**
Gözlem süresinde anlık enaz akım	**:**	**0.640**	**m3/sn**	**31.01.1996**

9. Anahtar Eğrisi (Seviyeler cm olarak)

Seviye	Akım	Seviye	Akım	Seviye	Akım	Seviye	Akım
134	0.459	158	5.5	183	17.8	208	42.3
138	1.2	163	7.2	188	21.4	213	50.2
143	2.0	168	9.3	193	25.7		
148	2.9	173	11.6	198	30.5		
153	4.1	178	14.5	203	35.9		

Akımlar 01 Ekim 2005 'den 30 Eylül 2006' a kadar m3/sn olarak

Gün	Ekim	Kasım	Aralık	Ocak	Şubat	Mart	Nisan	Mayıs	Haziran	Temmuz	Ağustos	Eylül
01	1.17	1.33	1.64	1.97	1.33	4.03	7.00	9.94	13.0	10.5	1.16	1.03
02	1.17	1.49	1.64	1.64	1.33	4.03	9.35	9.94	11.7	8.76	1.36	1.03
03	1.17	1.49	2.95	1.64	1.33	4.40	9.94	13.0	11.1	7.00	1.76	0.901
04	1.17	27.2	3.42	1.64	1.33	4.77	8.17	12.4	11.1	5.82	1.95	0.901
05	1.17	7.72	2.95	1.64	1.49	4.77	7.00	11.1	11.7	5.48	1.76	0.901
06	1.17	3.73	2.63	1.64	1.97	4.40	5.82	9.35	11.1	5.48	1.76	1.16
07	1.17	4.03	2.30	1.64	2.95	4.40	5.82	9.94	11.1	5.48	1.56	1.03
08	1.01	3.73	1.97	1.64	4.03	4.77	7.00	10.5	9.94	5.14	1.56	1.03
09	0.851	3.19	1.97	1.64	5.22	5.66	7.58	9.94	8.76	4.80	1.56	1.03
10	0.745	2.63	1.97	1.64	4.40	5.22	9.35	9.35	7.58	4.46	1.56	1.03
11	0.851	2.30	1.64	1.64	4.03	5.22	8.76	8.76	6.41	4.12	1.36	1.03
12	1.01	1.97	1.64	1.64	4.40	4.77	8.17	9.35	5.82	3.44	1.36	1.16
13	1.01	1.64	1.49	1.64	4.03	4.77	9.35	9.94	5.82	3.44	1.36	1.03
14	1.01	1.33	1.49	1.64	3.73	11.6	10.5	9.94	5.82	3.10	1.36	1.16
15	1.01	1.33	1.49	1.64	3.42	16.8	11.1	9.35	5.82	3.10	1.36	1.03
16	1.17	1.17	2.30	1.49	3.19	12.3	12.4	9.94	5.48	2.76	1.16	1.03
17	1.64	1.17	1.97	1.49	2.95	11.6	13.7	9.94	5.14	2.42	1.16	1.03
18	1.49	1.17	1.97	1.49	3.19	10.8	12.4	10.5	5.14	2.42	1.16	1.16
19	1.49	1.17	1.97	1.49	3.19	11.6	10.5	9.35	5.14	2.42	1.03	1.16
20	1.33	1.64	1.97	1.49	3.19	10.3	11.1	8.76	5.14	1.95	1.03	1.76
21	1.33	2.30	1.64	1.49	3.42	9.77	11.1	9.94	5.14	1.95	1.03	1.76
22	1.33	1.97	1.64	1.49	3.73	12.3	10.5	10.5	4.80	1.76	1.03	2.15
23	1.33	1.49	1.64	1.49	4.03	14.6	11.1	13.0	4.80	1.56	1.03	5.82
24	1.33	1.33	1.64	1.49	4.40	16.8	10.5	15.1	4.80	1.56	1.03	4.12
25	1.33	1.33	1.64	1.64	4.40	11.7	11.1	14.4	4.80	1.36	1.03	2.76
26	1.17	1.33	1.64	1.64	4.77	9.94	9.35	13.7	4.46	1.36	1.03	1.76
27	1.33	1.97	1.49	1.64	4.40	8.17	8.17	15.1	4.12	1.16	1.03	1.56
28	1.33	2.30	1.49	1.33	4.03	7.00	7.00	15.1	4.12	1.16	1.03	1.36
29	1.49	2.63	1.49	1.33	-----	6.41	7.00	14.4	7.00	1.16	1.03	1.16
30	1.49	2.30	1.49	1.33	-----	6.41	8.17	13.7	9.35	1.16	1.03	1.16
31	1.33	-----	1.49	1.33	-----	7.58	-----	13.7	-----	1.16	1.03	-----
Maks.	2.30	43.2	15.3	3.42	13.8	23.0	14.4	20.0	13.7	11.7	2.42	32.3
Min.	0.640	0.851	1.33	1.33	1.17	3.73	5.48	6.41	3.44	0.901	0.798	0.798
Ortalama	1.21	3.01	1.89	1.57	3.35	8.29	9.30	11.3	7.21	3.47	1.28	1.51
LT/SN/Km2	0.983	2.44	1.53	1.27	2.72	6.72	7.54	9.15	5.84	2.81	1.04	1.22
AKIM mm.	2.63	6.33	4.11	3.40	6.57	18.0	19.5	24.5	15.1	7.52	2.78	3.16
MİL. M3	3.25	7.81	5.07	4.20	8.11	22.2	24.1	30.2	18.7	9.28	3.43	3.91

SU YILI (2006) YILLIK TOPLAM AKIM 140.26 MİLYON M3 114 MM. 3.6 LT/SN/Km2

18. Seyhan Havzasi

D18A008 TACİN SUYU TACİN

YERİ : 1975BÜNYAN PINARBAŞI YOLUNU 12.3 KİLOMETRESİNDE SOLA AYRILAN HAMYOLUN 12.KM SİNDEKİ TACİN KÖYÜNDEDİR.
36°4'0" Doğu - 38°49'0" Kuzey

YAĞIŞ ALANI : 9,90 km2 **YAKLAŞIK KOT :** 1536 m

GÖZLEM SÜRESİ : 03.04.1964 - 30.09.2006

ORTALAMA AKIMLAR : Gözlem süresinde 1.010 m3/sn. (38 Yıllık) 2006 Su yılında 0.596 m3/sn.

ANLIK EN ÇOK VE EN AZ AKIMLAR:

2006 Su yılında anlık ençok akım	:	2.30	m3/sn	16.05.2006
2006 Su yılında anlık enaz akım	:	0.230	m3/sn	08.11.2005
Gözlem süresinde anlık ençok akım	:	6.30	m3/sn	13.06.1981
Gözlem süresinde anlık enaz akım	:	0.050	m3/sn	09.02.1975

14. Anahtar Eğrisi (Seviyeler cm olarak)

Seviye	Akım	Seviye	Akım
10	0.190	35	3.8
15	0.560	40	4.8
20	1.1	50	6.8
25	1.8		
30	2.7		

Akımlar 01 Ekim 2005 'den 30 Eylül 2006' a kadar m3/sn olarak

Gün	Ekim	Kasım	Aralık	Ocak	Şubat	Mart	Nisan	Mayıs	Haziran	Temmuz	Ağustos	Eylül
01	0.350	0.400	0.350	0.350	0.350	0.280	0.882	1.17	1.96	0.480	0.350	0.280
02	0.400	0.400	0.350	0.350	0.350	0.280	0.882	1.17	1.96	0.400	0.350	0.560
03	0.480	0.400	0.350	0.350	0.350	0.280	0.882	1.17	1.96	0.400	0.350	0.560
04	0.480	0.400	0.350	0.350	0.350	0.280	1.02	1.17	1.96	0.400	0.350	0.560
05	0.400	0.400	0.350	0.350	0.350	0.280	1.02	1.17	1.96	0.400	0.350	0.560
06	0.350	0.400	0.350	0.350	0.350	0.280	1.31	1.17	1.80	0.400	0.350	0.560
07	0.400	0.400	0.350	0.350	0.350	0.280	1.31	1.31	1.24	0.400	0.350	0.560
08	0.400	0.400	0.350	0.350	0.350	0.350	1.02	1.31	1.10	0.400	0.350	0.560
09	0.400	0.400	0.350	0.350	0.350	0.350	1.02	1.31	0.884	0.400	0.350	0.560
10	0.480	0.400	0.350	0.350	0.350	0.350	1.02	1.31	0.884	0.350	0.280	0.560
11	0.480	0.400	0.350	0.350	0.350	0.280	1.17	1.45	0.884	0.350	0.280	0.560
12	0.400	0.350	0.350	0.350	0.350	0.280	1.17	1.62	0.884	0.350	0.280	0.668
13	0.350	0.350	0.350	0.350	0.350	0.280	1.17	1.62	0.992	0.350	0.280	0.668
14	0.350	0.350	0.350	0.350	0.350	0.280	1.17	1.62	1.10	0.350	0.280	0.668
15	0.350	0.350	0.350	0.350	0.280	0.280	1.17	1.62	1.10	0.280	0.280	0.560
16	0.480	0.350	0.350	0.350	0.280	0.350	1.17	1.62	1.10	0.350	0.280	0.668
17	0.480	0.350	0.350	0.350	0.280	0.350	1.17	1.62	1.10	0.350	0.280	0.560
18	0.480	0.350	0.350	0.350	0.280	0.350	1.17	1.62	1.10	0.350	0.280	0.560
19	0.480	0.350	0.350	0.350	0.280	0.280	1.17	1.62	1.10	0.350	0.280	0.560
20	0.480	0.350	0.350	0.350	0.280	0.280	1.17	1.62	1.10	0.350	0.280	0.560
21	0.480	0.350	0.350	0.350	0.280	0.280	1.17	1.62	1.10	0.350	0.350	0.668
22	0.480	0.350	0.350	0.350	0.280	0.280	1.17	1.62	0.480	0.350	0.280	0.668
23	0.400	0.350	0.350	0.350	0.280	0.280	1.17	1.62	0.400	0.350	0.280	0.668
24	0.400	0.350	0.350	0.350	0.280	0.480	1.17	1.62	0.400	0.350	0.280	0.668
25	0.400	0.350	0.350	0.350	0.280	0.560	1.17	1.62	0.400	0.350	0.280	0.668
26	0.400	0.350	0.350	0.350	0.280	0.560	1.17	1.62	0.350	0.350	0.280	0.668
27	0.400	0.350	0.350	0.350	0.280	0.650	1.17	1.62	0.400	0.350	0.280	0.668
28	0.400	0.350	0.350	0.350	0.280	0.740	1.17	1.62	0.480	0.350	0.280	0.668
29	0.400	0.350	0.350	0.350	-----	0.882	1.17	1.79	0.480	0.350	0.280	0.668
30	0.400	0.350	0.350	0.350	-----	0.882	1.17	1.96	0.480	0.350	0.280	0.668
31	0.400	-----	0.350	0.350	-----	0.882	-----	1.96	-----	0.350	0.280	-----
Maks.	1.02	1.02	0.882	0.560	0.650	0.882	1.62	2.30	1.96	0.882	0.560	1.52
Min.	0.350	0.230	0.350	0.350	0.280	0.230	0.650	1.17	0.280	0.280	0.280	0.280
Ortalama	0.420	0.368	0.350	0.350	0.315	0.403	1.13	1.51	1.04	0.365	0.303	0.601
LT/SN/Km2	42.5	37.2	35.4	35.4	31.8	40.7	114.	153.	105.	36.9	30.6	60.7
AKIM mm.	114.	96.4	94.7	94.7	77.0	109.	295.	410.	272.	98.7	81.9	157.
MİL. M3	1.13	0.955	0.937	0.937	0.762	1.08	2.92	4.06	2.69	0.977	0.810	1.56

SU YILI (2006) YILLIK TOPLAM AKIM 18.82 MİLYON M3 1901 MM. 60.2 LT/SN/Km2

18. Seyhan Havzasi

D18A012 KÖRKÜN S. KAMIŞLI

YERİ : **ADANA - ÇAMARDI YOLUNUN 25 KM' SİNDE BULUNAN TAHTALI MEZAR KÖPRÜSÜNDEDİR.**
34°57'21" Doğu - 37°33'23" Kuzey

YAĞIŞ ALANI : **1065,00 km2** **YAKLAŞIK KOT : 1109 m**

GÖZLEM SÜRESİ : **09.09.1970 - 30.09.2006**

ORTALAMA AKIMLAR : **Gözlem süresinde 7.246 m3/sn. (35 Yıllık) 2006 Su yılında 2.677 m3/sn.**

ANLIK EN ÇOK VE EN AZ AKIMLAR:

2006 Su yılında anlık ençok akım	**:**	**18.6**	**m3/sn**	**04.11.2005**
2006 Su yılında anlık enaz akım	**:**	**0.299**	**m3/sn**	**22.09.2006**
Gözlem süresinde anlık ençok akım	**:**	**150.**	**m3/sn**	**04.10.1991**
Gözlem süresinde anlık enaz akım	**:**	**0.000**	**m3/sn**	**01.10.1995**

27. Anahtar Eğrisi (Seviyeler cm olarak)

Seviye	Akım	Seviye	Akım	Seviye	Akım	Seviye	Akım
38	0.124	90	5.8	160	42.0	210	87.5
42	0.207	110	12.6	170	50.0	220	98.0
46	0.330	130	22.2	180	58.5	230	109.
55	0.740	140	28.0	190	67.6	240	120.
70	2.1	150	34.8	200	77.3	250	131.

Akımlar 01 Ekim 2005 'den 30 Eylül 2006' a kadar m3/sn olarak

Gün	Ekim	Kasım	Aralık	Ocak	Şubat	Mart	Nisan	Mayıs	Haziran	Temmuz	Ağustos	Eylül
01	0.950	2.75	2.27	2.43	2.27	3.38	4.75	6.40	2.91	2.59	0.410	0.370
02	0.950	2.75	2.27	2.27	2.27	3.38	6.40	7.00	2.75	2.27	0.370	0.370
03	0.950	2.75	2.27	2.27	2.27	3.38	7.30	7.00	2.43	2.01	0.370	0.370
04	1.19	7.30	2.43	2.27	2.27	3.54	6.70	7.00	2.43	1.91	0.410	0.370
05	1.19	4.54	2.43	2.27	2.27	3.54	6.40	7.00	2.11	1.70	0.410	0.370
06	1.09	3.54	2.43	2.27	2.27	3.54	5.80	6.70	2.11	2.43	0.410	0.370
07	1.40	3.38	2.43	2.27	2.59	3.54	5.80	6.40	2.11	2.01	0.370	0.370
08	1.40	3.22	2.43	2.27	2.91	3.54	5.80	6.40	2.11	1.50	0.370	0.330
09	1.40	3.22	2.43	2.27	3.38	4.12	5.80	6.40	2.11	1.09	0.370	0.330
10	1.50	3.06	2.43	2.27	3.06	4.12	6.10	5.38	2.01	0.880	0.370	0.330
11	1.70	2.91	2.43	2.27	3.06	4.12	6.10	5.17	1.91	0.810	0.370	0.330
12	1.60	2.91	2.43	2.27	3.38	4.12	6.10	4.96	1.80	0.810	0.370	0.330
13	1.80	2.91	2.27	2.27	3.22	3.91	6.10	4.54	1.70	0.810	0.370	0.330
14	1.80	2.75	2.27	2.27	3.22	5.59	6.70	4.54	1.50	0.740	0.370	0.330
15	1.70	2.75	2.27	2.27	3.22	6.40	6.40	4.54	1.50	0.690	0.370	0.330
16	1.91	2.75	2.43	2.27	3.22	5.38	6.70	4.54	1.60	0.590	0.370	0.330
17	2.11	2.75	2.27	2.27	3.06	5.17	7.60	4.54	1.50	0.540	0.370	0.330
18	2.11	2.75	2.59	2.27	2.91	5.17	7.60	4.75	1.19	0.450	0.370	0.330
19	2.27	2.59	2.59	2.27	2.91	5.59	7.30	4.33	1.09	0.450	2.59	0.330
20	2.59	2.59	2.59	2.27	2.91	4.96	7.00	4.33	1.09	0.450	1.09	0.330
21	2.59	2.59	2.59	2.11	2.91	4.75	7.30	4.54	1.02	0.410	0.810	0.330
22	2.59	2.59	2.59	2.11	3.06	5.17	7.60	4.54	1.02	0.410	0.810	0.299
23	2.59	2.59	2.43	2.11	3.06	5.17	7.60	4.54	0.950	0.410	0.810	0.299
24	2.59	2.59	2.43	2.11	3.06	5.17	7.60	4.12	0.810	0.410	0.590	0.330
25	2.43	2.59	2.43	2.11	3.06	5.80	7.60	4.12	0.810	0.410	0.410	0.370
26	2.59	2.59	2.43	2.43	3.38	5.38	7.30	3.70	0.810	0.410	0.330	0.410
27	2.43	2.43	2.43	2.43	3.38	5.38	7.00	3.54	0.810	0.410	0.330	0.450
28	2.43	2.43	2.43	2.43	3.38	4.96	6.70	3.06	1.19	0.410	0.330	0.490
29	2.43	2.43	2.43	2.27	-----	4.75	6.40	3.06	1.80	0.410	0.410	0.590
30	2.27	2.43	2.43	2.27	-----	4.75	6.40	2.91	2.75	0.410	0.410	0.540
31	2.43	-----	2.43	2.27	-----	4.75	-----	2.75	-----	0.410	0.410	-----
Maks.	2.91	18.6	2.59	2.43	3.38	8.80	8.20	7.90	3.22	3.06	13.0	0.690
Min.	0.810	2.27	2.27	2.11	2.27	3.38	4.75	2.27	0.690	0.370	0.330	0.299
Ortalama	1.90	2.98	2.42	2.26	2.93	4.60	6.67	4.93	1.66	0.943	0.521	0.366
LT/SN/Km2	1.79	2.80	2.27	2.13	2.75	4.32	6.26	4.63	1.56	0.886	0.489	0.344
AKIM mm.	4.78	7.26	6.09	5.70	6.65	11.6	16.2	12.4	4.05	2.37	1.31	0.891
MİL. M3	5.10	7.73	6.48	6.07	7.08	12.3	17.3	13.2	4.31	2.53	1.40	0.949

SU YILI (2006) YILLIK TOPLAM AKIM 84.45 MİLYON M3 79 MM. 2.5 LT/SN/Km2

18. Seyhan Havzasi

D18A017 SARIZ SUYU DARIDERE

YERİ : 1987KAYSERİ K.MARAŞ YOLU ÜZERİNDE SARIZ KAVŞAĞINI GEÇTİKTENSONRA PETROL OFİSİNE 3 KM KALA KÖPRÜNÜN MANSABINDADIR.
36°28'0" Doğu - 38°27'0" Kuzey

YAĞIŞ ALANI : 315,60 km2 **YAKLAŞIK KOT :** 1542 m

GÖZLEM SÜRESİ : 01.07.1979 - 30.09.2006

ORTALAMA AKIMLAR : Gözlem süresinde 1.838 m3/sn. (23 Yıllık) 2006 Su yılında 1.401 m3/sn.

ANLIK EN ÇOK VE EN AZ AKIMLAR:

2006 Su yılında anlık ençok akım	:	13.9	m3/sn	08.03.2006
2006 Su yılında anlık enaz akım	:	0.340	m3/sn	11.08.2006
Gözlem süresinde anlık ençok akım	:	34.0	m3/sn	29.03.1983
Gözlem süresinde anlık enaz akım	:	0.070	m3/sn	01.10.2001

4. Anahtar Eğrisi (Seviyeler cm olarak)

Seviye	Akım	Seviye	Akım	Seviye	Akım	Seviye	Akım
6	0.070	16	0.540	40	3.3	70	9.6
8	0.118	18	0.700	45	4.2	80	12.2
10	0.197	20	0.860	50	5.0	90	15.1
12	0.290	30	1.9	55	6.0	100	18.2
14	0.400	35	2.6	60	7.2	130	25.0

Akımlar 01 Ekim 2005 'den 30 Eylül 2006' a kadar m3/sn olarak

Gün	Ekim	Kasım	Aralık	Ocak	Şubat	Mart	Nisan	Mayıs	Haziran	Temmuz	Ağustos	Eylül
01	0.700	0.958	0.860	0.860	0.860	1.35	4.49	2.55	1.57	0.780	0.540	0.470
02	0.700	0.958	0.860	0.860	0.860	1.57	4.49	2.70	1.46	0.780	0.620	0.540
03	0.700	0.958	0.860	0.860	0.700	2.29	4.32	3.00	1.35	0.700	0.540	0.540
04	0.700	1.06	0.860	0.780	0.860	3.47	4.15	2.70	1.15	0.700	0.540	0.540
05	0.700	1.15	0.860	0.860	0.860	3.30	3.81	3.00	1.06	0.700	0.540	0.540
06	0.700	1.06	0.860	0.860	0.958	3.64	3.30	3.00	1.06	0.780	0.540	0.540
07	0.700	1.06	0.780	0.860	0.958	4.83	3.30	3.00	0.958	0.780	0.540	0.540
08	0.700	0.958	0.780	0.860	1.06	8.38	3.15	3.00	0.958	0.700	0.470	0.540
09	0.700	0.958	0.860	0.958	0.958	6.27	3.15	3.15	1.06	0.620	0.470	0.540
10	0.700	0.958	0.860	0.958	0.958	4.49	3.15	2.70	1.06	0.620	0.340	0.540
11	0.700	0.958	0.780	0.958	0.958	3.64	3.00	2.29	1.06	0.620	0.340	0.540
12	0.700	0.860	0.780	1.06	1.06	3.64	3.00	2.29	0.860	0.620	0.340	0.540
13	0.700	0.860	0.780	1.06	1.06	4.49	3.00	2.16	0.780	0.620	0.340	0.400
14	0.700	0.860	0.780	0.780	1.06	5.21	3.00	2.16	0.780	0.780	0.340	0.400
15	0.860	0.860	0.780	0.700	0.958	4.66	3.00	2.16	0.780	0.780	0.340	0.470
16	0.958	0.860	0.958	0.860	0.958	4.15	2.85	2.16	0.780	0.700	0.400	0.470
17	1.15	0.860	0.958	1.06	1.06	3.64	2.85	2.55	0.860	0.620	0.340	0.470
18	1.06	0.860	0.958	0.860	1.06	3.64	2.85	2.42	0.860	0.540	0.340	0.470
19	1.06	0.860	1.06	0.780	1.06	3.64	2.85	2.29	0.860	0.540	0.400	0.470
20	1.06	0.860	1.15	0.700	0.958	3.64	2.70	2.29	0.860	0.540	0.540	0.470
21	0.958	0.958	1.06	0.700	1.06	4.15	2.70	2.29	0.860	0.620	0.540	0.470
22	0.860	0.958	1.06	0.700	0.958	4.66	2.70	2.16	0.780	0.540	0.470	0.470
23	0.860	0.860	1.06	0.700	0.958	3.81	2.70	2.16	0.780	0.620	0.470	0.470
24	0.860	0.958	0.958	0.780	0.958	4.15	2.70	2.03	0.780	0.620	0.470	0.700
25	0.958	0.860	0.860	0.780	1.06	4.66	2.70	2.03	0.780	0.540	0.400	0.700
26	0.860	0.860	0.860	0.780	1.15	4.83	2.70	1.79	0.780	0.540	0.400	0.780
27	0.860	0.860	1.06	0.780	1.25	5.21	2.55	1.90	0.860	0.540	0.400	0.700
28	0.860	0.860	1.15	0.700	1.35	5.42	2.55	1.79	0.780	0.540	0.400	0.620
29	0.860	0.860	1.06	0.860	-----	5.21	2.55	1.79	0.860	0.540	0.400	0.540
30	0.958	0.860	0.860	0.860	-----	5.63	2.55	1.68	0.780	0.540	0.400	0.620
31	0.958	-----	0.860	0.860	-----	4.66	-----	1.57	-----	0.540	0.400	-----
Maks.	1.15	1.46	1.25	1.35	1.46	13.9	4.49	3.15	1.68	0.958	0.860	0.780
Min.	0.700	0.700	0.780	0.620	0.620	1.35	0.700	0.700	0.400	0.470	0.340	0.400
Ortalama	0.832	0.922	0.912	0.840	0.999	4.27	3.09	2.35	0.940	0.635	0.439	0.537
LT/SN/Km2	2.64	2.92	2.89	2.66	3.16	13.5	9.80	7.44	2.98	2.01	1.39	1.70
AKIM mm.	7.06	7.58	7.74	7.13	7.66	36.2	25.4	19.9	7.72	5.39	3.73	4.41
MİL. M3	2.23	2.39	2.44	2.25	2.42	11.4	8.02	6.29	2.44	1.70	1.18	1.39

SU YILI (2006) YILLIK TOPLAM AKIM 44.15 MİLYON M3 140 MM. 4.4 LT/SN/Km2

18. Seyhan Havzasi

D18A018 İNDERESİ HASAN ÇAVUSLAR

YERİ MAHALLESINDEDIR : **KOZAN MANSURLU YOLUNUN 80 KM 'SİN DEKİ YUKARI KEÇELİ, KÖYÜNÜN HASANÇAVUŞLAR**

35°34'50" Doğu - 37°47'21" Kuzey

YAĞIŞ ALANI : **136,00 km2** **YAKLAŞIK KOT : 1400 m**

GÖZLEM SÜRESİ : **10.05.1982 - 30.09.2006**

ORTALAMA AKIMLAR : **Gözlem süresinde 2.166 m3/sn. (24 Yıllık) 2006 Su yılında 1.173 m3/sn.**

ANLIK EN ÇOK VE EN AZ AKIMLAR:

2006 Su yılında anlık ençok akım	**:**	**21.1**	**m3/sn**	**08.03.2006**
2006 Su yılında anlık enaz akım	**:**	**0.000**	**m3/sn**	**01.10.2005**
Gözlem süresinde anlık ençok akım	**:**	**175.**	**m3/sn**	**14.05.2001**
Gözlem süresinde anlık enaz akım	**:**	**0.000**	**m3/sn**	**27.07.1986**

Akımlar 01 Ekim 2005 'den 30 Eylül 2006' a kadar m3/sn olarak

Gün	Ekim	Kasım	Aralık	Ocak	Şubat	Mart	Nisan	Mayıs	Haziran	Temmuz	Ağustos	Eylül
01	KURU	KURU	0.350	0.389	0.315	6.00	3.54	0.970	0.174	0.425	0.174	0.112
02	KURU	KURU	0.315	0.389	0.151	6.83	8.81	0.970	0.112	0.389	0.151	0.112
03	KURU	KURU	0.284	0.350	0.151	8.81	9.45	0.970	0.174	0.389	0.151	0.093
04	KURU	0.174	0.257	0.350	0.151	9.13	6.83	0.900	0.257	0.389	0.257	0.078
05	KURU	0.350	0.257	0.315	0.151	7.38	7.38	0.843	0.284	1.90	0.227	0.078
06	KURU	0.174	0.227	0.315	0.257	6.55	6.27	0.784	0.284	1.20	0.197	0.078
07	KURU	0.130	0.197	0.315	0.666	7.11	5.28	0.725	0.227	0.843	0.174	0.078
08	KURU	0.112	0.197	0.284	1.05	12.7	4.85	0.725	0.227	0.666	0.174	0.078
09	KURU	0.078	0.174	0.257	0.843	12.0	4.85	1.05	0.227	0.561	0.151	0.078
10	KURU	0.050	0.174	0.257	0.843	7.94	4.85	0.900	0.227	0.425	0.151	0.078
11	KURU	0.030	0.174	0.257	1.72	5.50	4.19	0.843	0.227	0.425	0.151	0.078
12	KURU	0.023	0.174	0.257	2.44	5.07	3.76	0.784	0.227	0.425	0.151	0.078
13	KURU	0.011	0.174	0.227	1.99	5.07	3.27	0.725	0.257	0.389	0.130	0.093
14	KURU	KURU	0.151	0.227	1.54	6.83	2.86	0.725	0.284	0.389	0.130	0.093
15	0.023	KURU	0.174	0.197	1.36	8.81	2.58	0.666	0.350	0.315	0.030	0.078
16	0.023	KURU	0.197	0.197	1.54	7.38	2.31	0.606	0.284	0.315	0.023	0.093
17	0.064	KURU	0.197	0.174	1.63	6.55	2.44	0.666	0.227	0.315	0.030	0.093
18	0.030	KURU	0.284	0.151	0.970	6.00	3.54	0.666	0.197	0.315	0.030	0.093
19	0.011	KURU	1.99	0.174	0.900	5.07	3.13	0.606	0.174	0.284	0.039	0.093
20	KURU	0.078	3.76	0.257	0.900	4.19	1.54	0.561	0.151	0.284	0.050	0.093
21	KURU	1.12	2.08	0.315	0.970	3.54	1.45	0.516	0.151	0.350	0.030	0.093
22	KURU	0.843	1.63	0.350	1.20	3.27	1.36	0.516	0.174	0.284	0.011	0.112
23	KURU	0.606	1.27	0.227	1.54	3.54	1.36	0.468	0.174	0.257	0.023	0.112
24	KURU	0.468	1.05	0.151	1.90	4.63	1.45	0.389	0.174	0.284	0.030	0.130
25	KURU	0.389	0.784	0.151	2.58	10.7	1.54	0.350	0.174	0.284	0.078	0.151
26	KURU	0.350	0.725	0.151	3.40	8.21	1.20	0.350	0.151	0.227	0.112	0.151
27	KURU	0.350	0.606	0.174	5.28	6.55	1.12	0.315	0.151	0.197	0.112	0.151
28	KURU	0.350	0.516	0.666	2.44	5.28	1.05	0.315	0.174	0.174	0.130	0.130
29	KURU	0.350	0.516	0.725	-----	4.41	1.05	0.284	0.389	0.174	0.130	0.130
30	KURU	0.350	0.468	0.725	-----	3.98	0.970	0.284	0.516	0.174	0.130	0.130
31	KURU	-----	0.425	0.725	-----	3.76	-----	0.257	-----	0.151	0.112	-----
Maks.	0.197	1.81	5.72	1.45	6.27	21.1	14.1	1.05	0.516	7.11	0.315	0.151
Min.	KURU	KURU	0.130	0.151	0.130	3.13	0.970	0.227	0.093	0.151	KURU	0.064
Ortalama	0.005	0.213	0.638	0.313	1.39	6.54	3.48	0.636	0.227	0.426	0.112	0.101
LT/SN/Km2	0.036	1.57	4.69	2.30	10.2	48.1	25.6	4.68	1.67	3.13	0.823	0.745
AKIM mm.	0.096	4.06	12.6	6.16	24.7	129.	66.2	12.5	4.32	8.39	2.20	1.93
MİL. M3	0.013	0.552	1.71	0.838	3.36	17.5	9.01	1.70	0.587	1.14	0.300	0.262

SU YILI (2006) YILLIK TOPLAM AKIM 36.97 MİLYON M3 272 MM. 8.6 LT/SN/Km2

18. Seyhan Havzasi

D18A019 ASMACA Ç. FEKE

YERİ : **FEKE -MANSURLU YOLUNUN 2 KM SİNDEKİ ELEKTİRİK SANTRALI REGÜLATÖRÜNDEDIR.**
35°54'8" Doğu - 37°49'21" Kuzey

YAĞIŞ ALANI : **619,00 km2** **YAKLAŞIK KOT : 550 m**

GÖZLEM SÜRESİ : **01.06.1982 - 30.09.2006**

ORTALAMA AKIMLAR : **Gözlem süresinde 10.898 m3/sn. (24 Yıllık) 2006 Su yılında 8.697 m3/sn.**

ANLIK EN ÇOK VE EN AZ AKIMLAR:

2006 Su yılında anlık ençok akım	**:**	**51.5**	**m3/sn**	**19.12.2005**
2006 Su yılında anlık enaz akım	**:**	**2.38**	**m3/sn**	**08.10.2005**
Gözlem süresinde anlık ençok akım	**:**	**340.**	**m3/sn**	**02.07.1982**
Gözlem süresinde anlık enaz akım	**:**	**1.05**	**m3/sn**	**24.09.1985**

12. Anahtar Eğrisi (Seviyeler cm olarak)

Seviye	Akım	Seviye	Akım	Seviye	Akım	Seviye	Akım
30	2.1	40	4.8	100	34.6	190	98.6
32	2.6	44	6.5	120	46.8	200	108.
34	3.1	48	7.8	140	60.2	210	117.
36	3.6	60	12.5	160	74.9	220	126.
38	4.2	80	22.9	180	90.4	230	135.

Akımlar 01 Ekim 2005 'den 30 Eylül 2006' a kadar m3/sn olarak

Gün	Ekim	Kasım	Aralık	Ocak	Şubat	Mart	Nisan	Mayıs	Haziran	Temmuz	Ağustos	Eylül
01	2.58	2.58	3.74	4.61	4.31	17.9	27.4	12.8	5.81	4.61	3.07	2.58
02	2.58	2.79	3.74	4.31	4.31	19.1	30.7	12.8	5.81	4.31	3.07	2.79
03	2.58	2.79	3.74	4.31	4.31	26.1	28.0	12.8	5.81	4.01	3.07	2.79
04	2.58	3.74	3.27	4.31	4.31	30.0	24.1	12.4	5.81	4.01	3.07	2.79
05	2.58	3.74	3.27	4.31	4.31	24.8	23.5	11.9	5.49	4.01	3.07	2.79
06	2.58	3.07	3.27	4.01	5.81	22.2	22.2	11.9	5.49	4.01	3.07	2.79
07	2.58	2.79	3.27	4.01	18.5	22.2	22.9	11.4	5.16	3.74	3.07	2.79
08	2.38	2.79	3.27	4.01	25.4	28.0	23.5	11.0	5.16	3.74	3.07	2.79
09	2.38	2.79	3.27	4.01	22.2	36.7	24.1	12.4	5.16	3.47	3.07	2.79
10	2.38	2.79	3.27	4.01	18.5	31.3	30.0	11.9	5.16	3.47	3.07	2.79
11	2.38	2.79	3.27	4.01	33.3	25.4	29.3	11.4	5.16	3.47	3.07	2.79
12	2.38	2.79	3.27	3.74	37.3	22.2	28.0	11.0	5.16	3.47	3.07	3.27
13	2.38	2.79	3.07	3.74	35.3	20.9	26.7	11.0	5.16	3.47	3.07	3.27
14	2.38	2.79	3.07	3.74	28.7	22.9	26.7	10.5	5.16	3.47	3.07	3.27
15	2.38	2.79	3.07	3.74	22.2	25.4	25.4	9.59	5.16	3.47	3.07	3.27
16	3.07	2.79	3.74	3.74	16.6	24.1	25.4	9.59	5.16	3.47	3.07	3.27
17	5.49	2.79	4.89	3.47	13.7	22.2	25.4	9.59	5.16	3.47	3.07	3.07
18	3.27	2.79	7.14	3.47	11.9	22.9	23.5	9.59	5.16	3.47	3.07	3.07
19	3.47	2.79	40.7	3.47	11.0	24.8	21.6	9.17	4.89	3.47	3.07	3.07
20	2.79	3.27	25.4	4.31	10.5	22.2	20.3	9.17	4.89	3.27	3.07	2.79
21	2.58	8.32	13.3	3.74	10.5	20.9	19.7	8.74	4.89	3.27	3.07	2.79
22	2.58	7.14	9.17	3.74	10.5	19.7	19.1	8.32	4.61	3.27	3.07	2.79
23	2.58	5.16	7.89	3.74	12.4	19.1	18.5	8.32	4.31	3.27	3.07	3.07
24	2.58	4.31	6.81	3.74	12.4	23.5	17.9	7.89	4.31	3.27	3.07	3.27
25	2.58	4.01	6.14	4.31	12.4	40.7	17.3	7.47	4.31	3.27	2.79	3.27
26	2.58	3.74	5.81	5.49	14.8	36.0	16.0	7.14	4.31	3.27	2.79	3.47
27	2.38	3.74	5.49	6.14	17.9	30.7	14.8	7.14	4.31	3.27	2.79	3.47
28	2.38	3.74	5.16	5.49	18.5	28.0	13.7	6.81	4.31	3.27	2.79	3.47
29	2.38	3.74	4.89	4.89	-----	26.7	12.8	6.47	4.89	3.07	2.79	3.27
30	2.79	3.74	4.61	4.61	-----	26.7	12.8	6.14	5.16	3.07	2.58	3.27
31	2.58	-----	4.61	4.31	-----	27.4	-----	5.81	-----	3.07	2.58	-----
Maks.	6.81	10.1	51.5	6.14	38.7	45.4	31.3	12.8	5.81	4.61	3.07	3.74
Min.	2.38	2.58	2.79	3.47	4.31	17.3	12.8	5.81	4.31	3.07	2.58	2.58
Ortalama	2.68	3.53	6.63	4.18	15.8	25.5	22.4	9.75	5.04	3.52	2.99	3.03
LT/SN/Km2	4.33	5.70	10.7	6.75	25.5	41.2	36.1	15.7	8.15	5.69	4.84	4.90
AKIM mm.	11.6	14.8	28.7	18.1	61.7	110.	93.7	42.2	21.1	15.2	13.0	12.7
MİL. M3	7.19	9.15	17.8	11.2	38.2	68.3	58.0	26.1	13.1	9.44	8.02	7.86

SU YILI (2006) YILLIK TOPLAM AKIM 274.36 MİLYON M3 443 MM. 14.1 LT/SN/Km2

18. Seyhan Havzasi

D18A021 KAPUZ DERESİ KAPUZ

YERİ : YAHYALIYA 57 KM MESAFEDE KAPUZBAŞI ŞELALESİ ÜZERİNDEDİR.
35°24'0" Doğu - 37°46'20" Kuzey

YAĞIŞ ALANI : 394,50 km2 **YAKLAŞIK KOT** : 618 m

GÖZLEM SÜRESİ : 12.07.1984 - 30.09.2006

ORTALAMA AKIMLAR : Gözlem süresinde 7.810 m3/sn. (9 Yıllık) 2006 Su yılında 6.270 m3/sn.

ANLIK EN ÇOK VE EN AZ AKIMLAR:

2006 Su yılında anlık ençok akım	:	11.6	m3/sn	06.06.2006
2006 Su yılında anlık enaz akım	:	2.88	m3/sn	31.10.2005
Gözlem süresinde anlık ençok akım	:	28.3	m3/sn	11.12.1986
Gözlem süresinde anlık enaz akım	:	1.09	m3/sn	15.10.2001

3. Anahtar Eğrisi (Seviyeler cm olarak)

Seviye	Akım	Seviye	Akım	Seviye	Akım	Seviye	Akım
10	1.4	40	8.3	90	23.0	140	40.0
15	2.4	50	11.0	100	26.0		
20	3.6	60	14.0	110	29.5		
23	4.3	70	17.0	120	33.0		
30	5.9	80	20.0	130	36.5		

Akımlar 01 Ekim 2005 'den 30 Eylül 2006' a kadar m3/sn olarak

Gün	Ekim	Kasım	Aralık	Ocak	Şubat	Mart	Nisan	Mayıs	Haziran	Temmuz	Ağustos	Eylül
01	3.60	2.88	3.83	3.60	2.88	4.76	7.58	8.30	10.5	8.57	7.10	5.44
02	3.83	3.12	4.07	3.60	2.88	5.21	8.84	9.11	11.0	9.11	7.34	5.44
03	3.60	3.12	4.07	3.60	2.88	5.67	8.84	9.11	11.0	9.11	7.10	5.44
04	3.60	3.36	4.07	3.36	3.12	6.14	8.57	9.11	11.0	9.11	6.86	5.44
05	3.60	4.30	4.07	3.36	3.12	6.14	8.06	9.11	11.0	9.11	6.86	5.44
06	3.60	4.07	3.83	3.60	3.36	5.67	7.82	8.84	11.6	9.11	6.86	5.21
07	3.60	3.83	3.83	3.83	4.76	5.90	8.06	8.57	11.6	9.11	6.86	4.99
08	3.60	4.07	3.83	3.83	4.99	6.86	8.30	8.57	11.6	9.11	6.86	4.99
09	3.60	3.83	3.83	3.83	5.67	8.30	10.2	8.57	11.6	9.11	6.62	4.76
10	3.60	3.83	3.60	3.83	5.90	7.34	10.2	8.57	11.3	9.11	6.62	4.76
11	3.60	3.83	3.60	3.83	6.62	7.34	9.92	8.57	11.0	8.84	6.62	4.53
12	3.60	3.83	3.60	3.83	6.38	6.86	9.38	8.57	10.7	8.84	6.62	4.53
13	3.60	3.60	3.60	3.60	5.44	6.38	9.11	8.57	10.7	8.84	6.62	4.53
14	3.60	3.60	3.60	3.60	5.21	6.86	9.11	8.84	10.7	8.84	6.62	4.53
15	3.60	3.60	3.60	3.60	4.99	7.58	9.11	8.84	10.7	8.84	6.62	4.30
16	4.07	3.60	3.60	3.36	4.30	7.34	9.38	9.11	10.7	8.84	6.38	4.07
17	4.30	3.60	3.60	3.36	4.30	7.34	10.7	9.11	10.2	8.57	6.38	4.07
18	4.07	3.60	4.30	3.36	4.07	7.34	10.7	9.11	10.2	8.57	6.38	4.07
19	3.83	3.60	7.82	3.36	3.83	7.34	10.5	8.84	10.2	8.57	6.38	4.07
20	3.83	3.60	7.10	3.12	3.83	7.10	10.2	8.84	10.2	8.57	6.38	4.07
21	3.60	5.44	5.44	3.12	3.83	6.62	10.2	9.65	10.2	8.57	6.38	4.07
22	3.60	5.67	4.76	3.12	4.07	6.62	10.2	9.65	9.92	8.57	6.14	4.07
23	3.60	4.99	4.53	3.12	4.30	6.86	10.2	9.65	9.38	8.30	6.14	4.07
24	3.60	4.53	4.30	2.88	4.30	7.58	10.2	9.92	9.38	8.30	6.14	4.07
25	3.60	4.53	4.30	3.12	4.53	9.92	9.92	9.92	9.11	8.30	5.90	4.07
26	3.60	4.30	4.07	3.36	4.53	8.84	9.92	10.2	9.11	8.06	5.90	4.07
27	3.60	4.30	4.07	3.36	4.76	8.30	9.38	10.5	9.11	8.06	5.90	4.07
28	3.60	4.30	4.07	3.36	4.30	8.30	9.11	10.5	9.11	7.82	5.90	4.07
29	3.36	4.30	3.83	3.12	-----	8.06	9.11	10.7	9.11	7.58	5.67	4.07
30	3.36	3.60	3.83	3.12	-----	8.06	8.06	10.7	8.06	7.58	5.67	3.36
31	2.88	-----	3.36	2.88	-----	7.34	-----	9.92	-----	6.62	5.21	-----
Maks.	4.30	7.34	8.30	3.83	7.10	10.2	11.0	11.0	11.6	9.11	7.34	5.67
Min.	2.88	2.88	3.36	2.88	2.88	4.76	7.58	8.30	8.06	6.62	5.21	3.36
Ortalama	3.64	3.96	4.19	3.42	4.40	7.10	9.36	9.28	10.3	8.57	6.42	4.49
LT/SN/Km2	9.22	10.0	10.6	8.67	11.1	18.0	23.7	23.5	26.2	21.7	16.3	11.4
AKIM mm.	24.7	26.0	28.5	23.2	27.0	48.2	61.5	63.0	67.9	58.2	43.6	29.5
MİL. M3	9.74	10.3	11.2	9.16	10.6	19.0	24.3	24.8	26.8	23.0	17.2	11.6

SU YILI (2006) YILLIK TOPLAM AKIM 197.70 MİLYON M3 501 MM. 15.9 LT/SN/Km2

18. Seyhan Havzasi

D18A022 AKSU Ç. B.SOFULU

YERİ : **ALADAĞ İLÇESİ POSORMANLARI MEVKİİNDE KICAK - BÜYÜK SOFULU KÖYLERİ ARASINDAKİ KÖPRÜDEDİR**
35°12'22" Doğu - 37°34'4" Kuzey

YAĞIŞ ALANI : **98,00 km2** **YAKLAŞIK KOT : 960 m**

GÖZLEM SÜRESİ : **12.09.1985 - 30.09.2006**

ORTALAMA AKIMLAR : **Gözlem süresinde 1.988 m3/sn. (16 Yıllık) 2006 Su yılında 1.204 m3/sn.**

ANLIK EN ÇOK VE EN AZ AKIMLAR:

2006 Su yılında anlık ençok akım	:	**8.10**	**m3/sn**	**04.11.2005**
2006 Su yılında anlık enaz akım	:	**0.000**	**m3/sn**	**11.09.2006**
Gözlem süresinde anlık ençok akım	:	**52.5**	**m3/sn**	**29.11.1989**
Gözlem süresinde anlık enaz akım	:	**0.000**	**m3/sn**	**16.09.1997**

Akımlar 01 Ekim 2005 'den 30 Eylül 2006' a kadar m3/sn olarak

Gün	Ekim	Kasım	Aralık	Ocak	Şubat	Mart	Nisan	Mayıs	Haziran	Temmuz	Ağustos	Eylül
01	0.319	0.381	0.984	0.984	0.734	2.55	4.06	2.14	0.651	0.506	0.036	0.016
02	0.205	0.381	0.901	0.901	0.734	2.82	5.63	2.14	0.568	0.506	0.036	0.016
03	0.124	0.734	0.901	0.818	0.734	2.82	4.06	2.14	0.568	0.506	0.036	0.016
04	0.257	6.48	0.901	0.818	0.734	3.17	4.06	2.14	0.568	0.506	0.036	KURU
05	0.161	2.82	0.818	0.818	0.734	3.17	3.84	1.85	0.568	0.568	0.036	KURU
06	0.161	2.41	0.818	0.818	0.734	2.95	3.84	1.85	0.568	0.568	0.036	KURU
07	0.205	2.68	0.734	0.818	0.818	3.17	3.84	1.57	0.568	0.568	0.036	KURU
08	0.205	2.68	0.651	0.818	0.984	3.17	3.84	0.984	0.568	0.568	0.036	KURU
09	0.124	2.28	0.651	0.734	1.22	3.62	3.84	0.818	0.568	0.568	0.036	KURU
10	0.036	2.14	0.568	0.734	1.57	3.39	4.06	0.651	0.568	0.568	0.059	KURU
11	0.036	1.34	0.568	0.651	2.14	3.39	3.84	0.651	0.319	0.568	0.059	KURU
12	0.036	1.10	0.568	0.651	2.41	3.39	3.62	0.651	0.319	0.568	0.036	KURU
13	0.088	1.10	0.506	0.568	2.28	3.39	3.62	0.651	0.319	0.568	0.036	KURU
14	0.088	0.984	0.506	0.568	2.14	3.84	3.62	0.651	0.319	0.568	0.016	KURU
15	0.161	0.984	0.568	0.568	2.00	4.26	3.62	0.651	0.319	0.568	0.016	KURU
16	0.381	0.984	0.568	0.568	2.00	4.26	3.62	0.651	0.319	0.568	0.016	KURU
17	0.901	0.901	0.568	0.568	2.00	4.26	3.62	0.651	0.319	0.319	0.036	KURU
18	0.568	0.901	1.34	0.568	1.85	4.45	3.62	0.651	0.319	0.257	0.059	KURU
19	0.444	1.34	3.39	0.568	1.71	4.26	3.17	0.651	0.319	0.257	0.059	KURU
20	0.444	2.41	2.68	0.734	1.71	4.26	3.17	0.651	0.319	0.257	0.016	0.016
21	0.444	2.55	2.14	0.734	1.71	4.26	3.17	0.651	0.319	0.257	0.016	0.016
22	0.444	2.14	2.00	0.734	1.85	4.26	3.17	0.651	0.319	0.257	0.016	KURU
23	0.444	1.45	1.85	0.734	2.14	4.26	2.82	0.651	0.319	0.161	0.016	KURU
24	0.444	1.22	1.71	0.734	2.55	4.45	2.55	0.651	0.319	0.088	0.016	KURU
25	0.444	0.984	1.45	0.734	2.55	5.24	2.55	0.651	0.319	0.088	0.016	0.016
26	0.444	0.984	1.34	0.734	2.55	4.84	2.28	0.651	0.319	0.088	0.016	0.036
27	0.444	0.984	1.22	0.734	2.55	4.26	2.28	0.651	0.381	0.088	0.016	0.036
28	0.444	0.984	1.10	0.734	2.41	4.26	2.28	0.651	0.568	0.088	0.016	0.036
29	0.444	0.984	0.984	0.734	-----	4.06	2.28	0.651	0.568	0.088	0.016	0.036
30	0.444	0.984	0.984	0.734	-----	4.06	2.28	0.651	0.568	0.088	0.016	0.124
31	0.444	-----	0.984	0.734	-----	4.06	-----	0.651	-----	0.088	0.016	-----
Maks.	1.22	8.10	4.65	0.984	2.82	5.63	5.82	2.41	2.55	0.818	0.059	0.161
Min.	0.016	0.381	0.506	0.568	0.734	2.41	2.14	0.651	0.257	0.088	0.016	KURU
Ortalama	0.317	1.61	1.13	0.721	1.70	3.83	3.41	0.966	0.432	0.365	0.029	0.012
LT/SN/Km2	3.24	16.4	11.5	7.36	17.3	39.0	34.8	9.86	4.41	3.72	0.299	0.124
AKIM mm.	8.66	42.6	30.8	19.7	41.9	105.	90.1	26.4	11.4	9.97	0.801	0.321
MİL. M3	0.849	4.17	3.02	1.93	4.11	10.2	8.83	2.59	1.12	0.977	0.078	0.031

SU YILI (2006) YILLIK TOPLAM AKIM 37.90 MİLYON M3 387 MM. 12.3 LT/SN/Km2

18. Seyhan Havzasi

D18A023 YAĞDEĞLEME Ç. YENİKÖY

YERİ : **ALADAĞ İLÇESİ POSORMANLARI MEVKİİNDE YENİKÖY'E GELMEDEN ÖNCEKİ KÖPRÜDEDİR.**
35°15'24" Doğu - 37°32'2" Kuzey

YAĞIŞ ALANI : **23,50 km2** **YAKLAŞIK KOT : 870 m**

GÖZLEM SÜRESİ : **12.09.1985 - 30.09.2006**

ORTALAMA AKIMLAR : **Gözlem süresinde 0.400 m3/sn. (21 Yıllık) 2006 Su yılında 0.173 m3/sn.**

ANLIK EN ÇOK VE EN AZ AKIMLAR:

2006 Su yılında anlık ençok akım	**:**	**8.68**	**m3/sn**	**29.06.2006**
2006 Su yılında anlık enaz akım	**:**	**0.000**	**m3/sn**	**14.10.2005**
Gözlem süresinde anlık ençok akım	**:**	**23.0**	**m3/sn**	**09.01.1987**
Gözlem süresinde anlık enaz akım	**:**	**0.000**	**m3/sn**	**01.10.1985**

Akımlar 01 Ekim 2005 'den 30 Eylül 2006' a kadar m3/sn olarak

Gün	Ekim	Kasım	Aralık	Ocak	Şubat	Mart	Nisan	Mayıs	Haziran	Temmuz	Ağustos	Eylül
01	KURU	KURU	0.158	0.096	0.390	0.468	0.468	0.072	0.045	0.057	KURU	KURU
02	KURU	KURU	0.158	0.096	0.390	0.390	0.546	0.072	0.045	0.057	KURU	KURU
03	KURU	KURU	0.158	0.057	0.312	0.390	0.546	0.072	0.033	0.072	KURU	KURU
04	KURU	0.018	0.120	0.057	0.234	0.390	0.546	0.045	0.033	0.072	KURU	KURU
05	KURU	0.010	0.120	0.045	0.234	0.390	0.546	0.045	0.025	0.057	KURU	KURU
06	KURU	0.007	0.120	0.045	0.234	0.390	0.546	0.057	0.025	0.007	KURU	KURU
07	KURU	0.005	0.120	0.045	0.390	0.390	0.468	0.057	0.025	0.002	KURU	KURU
08	KURU	0.005	0.057	0.045	0.846	0.468	0.468	0.057	0.025	0.002	KURU	KURU
09	KURU	0.003	0.057	0.045	1.34	0.958	0.390	0.057	0.025	0.001	KURU	KURU
10	KURU	0.002	0.057	0.033	0.958	0.735	0.390	0.057	0.025	0.001	KURU	KURU
11	KURU	0.002	0.057	0.033	0.735	0.735	0.468	0.045	0.025	0.001	KURU	KURU
12	KURU	KURU	0.045	0.033	0.735	0.546	0.468	0.045	0.018	0.001	KURU	KURU
13	KURU	KURU	0.045	0.033	0.735	0.624	0.390	0.045	0.018	0.001	KURU	KURU
14	KURU	KURU	0.045	0.033	0.624	0.958	0.390	0.045	0.014	0.001	KURU	KURU
15	KURU	KURU	0.045	0.018	0.624	0.958	0.312	0.045	0.014	0.001	KURU	KURU
16	KURU	KURU	0.045	0.018	0.624	1.07	0.312	0.045	0.010	0.001	KURU	KURU
17	KURU	0.001	0.045	0.018	0.624	1.18	0.196	0.045	0.010	0.001	KURU	KURU
18	KURU	0.001	0.072	0.018	0.624	1.18	0.196	0.033	0.010	KURU	KURU	KURU
19	KURU	0.002	1.07	0.018	0.624	1.18	0.158	0.033	0.007	KURU	KURU	KURU
20	KURU	0.033	0.624	0.057	0.624	1.07	0.158	0.033	0.007	KURU	KURU	KURU
21	KURU	0.158	0.468	0.057	0.546	0.846	0.120	1.51	0.007	KURU	KURU	KURU
22	KURU	0.196	0.390	0.072	0.546	0.735	0.120	0.234	0.007	KURU	KURU	KURU
23	KURU	0.196	0.234	0.072	0.546	0.735	0.120	0.096	0.007	KURU	KURU	KURU
24	KURU	0.196	0.234	0.096	0.546	0.735	0.096	0.096	0.005	KURU	KURU	KURU
25	KURU	0.196	0.234	0.158	0.546	0.624	0.096	0.096	0.005	KURU	KURU	KURU
26	KURU	0.196	0.234	0.312	0.546	0.624	0.096	0.072	0.005	KURU	KURU	KURU
27	KURU	0.196	0.196	0.234	0.468	0.546	0.096	0.072	0.005	KURU	KURU	KURU
28	KURU	0.196	0.196	0.234	0.468	0.546	0.096	0.057	0.005	KURU	KURU	KURU
29	KURU	0.158	0.158	0.390	-----	0.546	0.072	0.057	1.51	KURU	KURU	KURU
30	KURU	0.158	0.120	0.390	-----	0.468	0.072	0.057	0.158	KURU	KURU	KURU
31	KURU	-----	0.120	0.390	-----	0.468	-----	0.045	-----	KURU	KURU	-----
Maks.	KURU	0.196	1.67	0.468	1.51	1.18	0.624	6.52	8.68	0.158	KURU	KURU
Min.	KURU	KURU	0.045	0.018	0.234	0.390	0.072	0.033	0.005	KURU	KURU	KURU
Ortalama	KURU	0.064	0.187	0.105	0.575	0.688	0.298	0.110	0.072	0.011	KURU	KURU
LT/SN/Km2	0.000	2.74	7.96	4.46	24.5	29.3	12.7	4.66	3.05	0.460	0.000	0.000
AKIM mm.	0.000	7.11	21.3	11.9	59.2	78.5	32.9	12.5	7.92	1.23	0.000	0.000
MİL. M3	0.000	0.167	0.501	0.281	1.39	1.84	0.773	0.294	0.186	0.029	0.000	0.000

SU YILI (2006) YILLIK TOPLAM AKIM 5.46 MİLYON M3 232 MM. 7.4 LT/SN/Km2

18. Seyhan Havzasi

D18A027 Ecemis Ç. Elekgölü

YERİ : **NİĞDE ELEKGÖLÜ KÖYÜ**
35°0'56" Doğu - 37°46'21" Kuzey

YAĞIŞ ALANI : **1833,00 km2** **YAKLAŞIK KOT : 1550 m**

GÖZLEM SÜRESİ : **01.10.1986 - 30.09.2006**

ORTALAMA AKIMLAR : **Gözlem süresinde 3.200 m3/sn. (19 Yıllık) 2006 Su yılında 1.849 m3/sn.**

ANLIK EN ÇOK VE EN AZ AKIMLAR:

2006 Su yılında anlık ençok akım	**:**	**14.6**	**m3/sn**	**19.08.2006**
2006 Su yılında anlık enaz akım	**:**	**0.220**	**m3/sn**	**14.09.2006**
Gözlem süresinde anlık ençok akım	**:**	**32.0**	**m3/sn**	**13.06.1999**
Gözlem süresinde anlık enaz akım	**:**	**0.170**	**m3/sn**	**01.10.2001**

İstasyon için kullanılmış anahtar bulunamadı.

Akımlar 01 Ekim 2005 'den 30 Eylül 2006' a kadar m3/sn olarak

Gün	Ekim	Kasım	Aralık	Ocak	Şubat	Mart	Nisan	Mayıs	Haziran	Temmuz	Ağustos	Eylül
01	0.900	1.86	2.13	2.04	2.04	1.95	2.31	3.92	2.78	1.41	0.324	0.300
02	0.900	1.86	2.13	1.86	2.04	1.86	2.78	4.11	2.78	1.31	0.324	0.300
03	0.900	1.86	2.04	1.68	1.95	1.86	2.78	4.30	2.78	1.11	0.368	0.300
04	0.900	1.86	1.95	1.77	1.95	1.77	2.59	4.11	2.59	1.02	0.368	0.260
05	0.900	1.86	1.95	1.86	1.95	1.68	2.40	4.11	2.40	1.21	0.368	0.260
06	0.900	1.95	1.95	1.95	1.95	1.68	2.40	4.30	2.22	1.21	0.324	0.260
07	0.900	1.95	2.04	2.04	1.95	1.68	2.40	4.30	2.22	0.918	0.280	0.260
08	0.900	1.95	2.04	2.04	1.95	1.77	2.59	4.30	2.13	0.756	0.280	0.260
09	0.900	1.95	2.04	2.04	1.95	1.77	2.59	4.30	2.13	0.692	0.280	0.260
10	0.900	1.95	2.13	2.04	1.95	1.77	2.59	4.30	2.04	0.692	0.280	0.260
11	1.00	2.04	2.22	1.95	1.95	1.86	2.59	4.11	2.04	0.628	0.280	0.260
12	1.00	2.04	2.22	2.04	1.95	1.86	2.59	3.92	1.95	0.628	0.280	0.260
13	1.00	2.04	2.22	2.13	1.86	1.86	2.78	3.92	1.95	0.628	0.252	0.260
14	1.00	2.04	2.22	2.13	1.86	1.95	3.16	3.92	1.86	0.564	0.252	0.260
15	1.10	2.04	2.22	2.13	1.86	2.04	3.35	3.92	1.77	0.500	0.252	0.260
16	1.10	2.04	2.22	2.13	1.86	2.04	3.73	3.92	1.77	0.456	0.224	0.260
17	1.20	2.04	2.22	2.13	1.95	2.13	3.92	4.93	1.77	0.412	0.224	0.260
18	1.30	2.04	2.22	2.13	1.95	2.13	4.11	5.14	1.77	0.412	0.456	0.260
19	1.59	2.04	2.22	2.13	1.95	2.13	3.92	4.72	1.68	0.412	5.14	0.260
20	1.77	2.04	2.22	2.13	1.95	2.13	3.73	4.30	1.59	0.412	0.900	0.260
21	1.77	2.04	2.22	2.13	1.95	2.13	4.30	4.30	1.50	0.368	0.600	0.260
22	1.86	2.13	2.22	2.13	2.04	2.13	4.30	4.11	1.40	0.368	0.500	0.260
23	1.95	2.13	2.22	2.04	2.04	2.13	4.93	3.92	1.20	0.324	0.460	0.260
24	1.95	2.13	2.22	2.04	2.04	2.13	4.93	3.73	1.10	0.324	0.380	0.300
25	1.95	2.13	2.22	2.04	2.04	2.13	4.51	3.73	1.10	0.324	0.340	0.300
26	1.86	2.13	2.22	1.95	2.13	2.22	4.51	3.73	1.10	0.324	0.340	0.300
27	1.77	2.13	2.22	1.95	2.13	2.22	4.30	3.54	1.10	0.324	0.300	0.300
28	1.77	2.13	2.22	2.04	2.04	2.22	3.92	3.54	1.10	0.324	0.300	0.300
29	1.77	2.13	2.22	2.04	-----	2.22	3.92	3.35	1.30	0.324	0.300	0.300
30	1.86	2.13	2.22	2.04	-----	2.13	3.92	3.35	1.90	0.324	0.300	0.300
31	1.86	-----	2.22	2.04	-----	2.13	-----	3.16	-----	0.324	0.300	-----
Maks.	1.95	2.13	2.31	2.31	2.13	2.31	5.14	5.35	2.78	1.41	14.6	0.300
Min.	0.900	1.86	1.95	1.68	1.86	1.59	2.22	3.16	1.00	0.280	0.224	0.220
Ortalama	1.34	2.02	2.16	2.03	1.97	1.99	3.43	4.04	1.83	0.614	0.502	0.273
LT/SN/Km2	0.729	1.10	1.18	1.11	1.08	1.09	1.87	2.21	1.00	0.335	0.274	0.149
AKIM mm.	1.95	2.86	3.16	2.96	2.60	2.91	4.85	5.91	2.59	0.897	0.734	0.387
MİL. M3	3.58	5.24	5.79	5.43	4.77	5.33	8.89	10.8	4.75	1.64	1.35	0.708

SU YILI (2006) YILLIK TOPLAM AKIM 58.28 MİLYON M3 32 MM. 1.0 LT/SN/Km2

18. Seyhan Havzasi

D18A028 Ecemis Ç. ÇUKURBAĞ

YERİ : **ÇAMARDI ÇUKURBAĞ KÖYÜ**
35°2'59" Doğu - 37°50'12" Kuzey

YAĞIŞ ALANI : **339,00 km2** **YAKLAŞIK KOT : 1600 m**

GÖZLEM SÜRESİ : **23.06.1988 - 30.09.2006**

ORTALAMA AKIMLAR : **Gözlem süresinde 1.829 m3/sn. (16 Yıllık) 2006 Su yılında 0.879 m3/sn.**

ANLIK EN ÇOK VE EN AZ AKIMLAR:

2006 Su yılında anlık ençok akım	**:**	**31.7**	**m3/sn**	**18.08.2006**
2006 Su yılında anlık enaz akım	**:**	**0.003**	**m3/sn**	**08.09.2006**
Gözlem süresinde anlık ençok akım	**:**	**31.7**	**m3/sn**	**18.08.2006**
Gözlem süresinde anlık enaz akım	**:**	**0.000**	**m3/sn**	**10.09.1991**

İstasyon için kullanılmış anahtar bulunamadı.

Akımlar 01 Ekim 2005 'den 30 Eylül 2006' a kadar m3/sn olarak

Gün	Ekim	Kasım	Aralık	Ocak	Şubat	Mart	Nisan	Mayıs	Haziran	Temmuz	Ağustos	Eylül
01	0.102	0.864	0.734	0.981	0.668	0.668	0.864	2.66	2.66	0.538	0.056	0.022
02	0.093	0.864	0.734	0.981	0.668	0.668	0.981	3.05	2.10	0.538	0.056	0.022
03	0.102	0.799	0.799	0.981	0.668	0.668	1.22	3.05	1.94	0.538	0.048	0.018
04	0.102	0.734	0.864	0.981	0.668	0.734	1.33	2.85	1.94	0.407	0.048	0.018
05	0.102	0.734	0.864	0.981	0.734	0.734	1.33	2.85	1.61	0.407	0.074	0.029
06	0.102	0.799	0.981	0.864	0.734	0.734	1.33	2.85	1.33	0.407	0.083	0.004
07	0.112	0.734	0.799	0.864	0.734	0.668	1.22	2.85	1.22	0.342	0.083	0.004
08	0.112	0.734	0.799	0.864	0.734	0.668	1.22	2.85	1.10	0.211	0.074	0.003
09	0.132	0.799	0.734	0.864	0.734	0.734	1.33	3.05	0.981	0.191	0.102	0.003
10	0.152	0.734	0.734	0.864	0.734	0.734	1.33	2.85	0.981	0.171	0.112	0.003
11	0.171	0.734	0.734	0.864	0.734	0.799	1.77	2.66	0.981	0.152	0.083	0.003
12	0.191	0.734	0.734	0.864	0.734	0.799	1.77	3.05	0.799	0.132	0.074	0.004
13	0.211	0.734	0.734	0.864	0.734	0.734	1.94	3.05	0.668	0.132	0.064	0.008
14	0.276	0.864	0.734	0.864	0.734	0.799	2.10	3.05	0.668	0.132	0.093	0.004
15	0.342	0.864	0.734	0.734	0.734	0.799	2.10	3.05	0.668	0.112	0.093	0.011
16	0.342	0.864	0.734	0.734	0.668	0.799	2.46	3.51	0.668	0.112	0.102	0.004
17	0.473	0.864	0.734	0.734	0.668	0.799	3.25	3.51	0.538	0.112	0.083	0.008
18	0.473	0.864	0.734	0.734	0.668	0.799	3.05	3.25	0.473	0.112	0.131	0.004
19	0.538	0.799	0.734	0.734	0.668	0.799	2.66	3.05	0.407	0.102	0.398	0.004
20	0.603	0.734	0.734	0.734	0.668	0.799	2.66	2.85	0.276	0.102	0.066	0.004
21	0.734	0.734	0.734	0.734	0.668	0.799	3.25	2.85	0.211	0.102	0.022	0.004
22	0.799	0.734	0.799	0.734	0.668	0.799	3.25	2.66	0.211	0.102	0.018	0.004
23	0.864	0.734	0.864	0.668	0.668	0.799	3.25	3.05	0.211	0.093	0.018	0.004
24	1.10	0.734	0.864	0.668	0.668	0.799	3.05	3.25	0.191	0.093	0.018	0.004
25	1.10	0.734	0.864	0.668	0.668	0.799	2.85	3.25	0.191	0.093	0.018	0.004
26	1.22	0.734	0.864	0.668	0.668	0.799	2.85	3.25	0.171	0.093	0.018	0.004
27	1.33	0.734	0.864	0.668	0.668	0.799	2.46	3.25	0.171	0.093	0.018	0.008
28	1.22	0.734	0.864	0.668	0.668	0.864	2.26	3.25	0.171	0.083	0.018	0.004
29	1.10	0.734	0.864	0.668	-----	0.864	2.26	3.05	0.191	0.083	0.022	0.008
30	0.864	0.734	0.864	0.668	-----	0.864	2.26	2.66	0.538	0.074	0.022	0.011
31	0.864	-----	0.864	0.668	-----	0.864	-----	2.46	-----	0.064	0.022	-----
Maks.	1.33	0.864	1.33	0.981	0.799	0.981	3.76	3.76	3.05	0.538	31.7	0.029
Min.	0.093	0.734	0.734	0.603	0.668	0.668	0.864	2.46	0.171	0.064	0.018	0.003
Ortalama	0.514	0.773	0.796	0.792	0.694	0.774	2.12	3.00	0.809	0.191	0.069	0.008
LT/SN/Km2	1.52	2.28	2.35	2.34	2.05	2.28	6.26	8.84	2.39	0.564	0.203	0.023
AKIM mm.	4.06	5.91	6.29	6.26	4.95	6.11	16.2	23.7	6.18	1.51	0.545	0.060
MİL. M3	1.38	2.00	2.13	2.12	1.68	2.07	5.50	8.03	2.10	0.512	0.185	0.020

SU YILI (2006) YILLIK TOPLAM AKIM 27.73 MİLYON M3 82 MM. 2.6 LT/SN/Km2

18. Seyhan Havzasi

D18A032 SARIZ D. ŞARKÖY

YERİ : **ADANA İLİ TUFANBEYLİ İLÇESİNE BAĞLI ŞARKÖY' ÜNDEDİR.**
36°19'26" Doğu - 38°19'54" Kuzey

YAĞIŞ ALANI : **754,20 km2** **YAKLAŞIK KOT : 1400 m**

GÖZLEM SÜRESİ : **01.01.1988 - 30.09.2006**

ORTALAMA AKIMLAR : **Gözlem süresinde 4.302 m3/sn. (14 Yıllık) 2006 Su yılında 3.891 m3/sn.**

ANLIK EN ÇOK VE EN AZ AKIMLAR:

2006 Su yılında anlık ençok akım	:	**38.4**	**m3/sn**	**08.03.2006**
2006 Su yılında anlık enaz akım	:	**1.31**	**m3/sn**	**24.10.2005**
Gözlem süresinde anlık ençok akım	:	**52.1**	**m3/sn**	**06.03.2004**
Gözlem süresinde anlık enaz akım	:	**0.000**	**m3/sn**	**01.10.1995**

55. Anahtar Eğrisi (Seviyeler cm olarak)

Seviye	Akım	Seviye	Akım	Seviye	Akım	Seviye	Akım
15	0.394	75	1.5	205	4.0	281	5.5
23	0.542	115	2.2	219	4.2	300	5.9
31	0.687	155	3.0	235	4.6	313	6.1
39	0.835	176	3.4	252	4.9	331	6.5
47	0.979	191	3.7	268	5.2		

Akımlar 01 Ekim 2005 'den 30 Eylül 2006' a kadar m3/sn olarak

Gün	Ekim	Kasım	Aralık	Ocak	Şubat	Mart	Nisan	Mayıs	Haziran	Temmuz	Ağustos	Eylül
01	1.67	1.92	2.16	2.25	1.67	3.10	14.0	6.87	2.76	2.16	1.59	1.59
02	1.67	1.92	2.16	2.25	1.59	3.94	16.0	6.87	2.64	2.16	1.59	1.59
03	1.67	1.92	2.16	2.25	1.67	7.10	15.3	7.10	2.53	2.08	1.59	1.59
04	1.67	1.92	2.16	2.00	1.59	16.0	13.0	6.64	2.25	2.16	1.59	1.59
05	1.67	2.53	2.16	1.92	1.52	15.8	12.0	6.17	2.16	2.08	1.59	1.59
06	1.52	2.41	2.16	1.92	1.59	17.3	11.5	5.71	2.16	2.16	1.59	1.59
07	1.52	2.25	2.16	1.92	1.92	20.0	11.0	5.48	2.33	2.16	1.59	1.59
08	1.52	2.25	2.16	1.92	2.16	30.8	11.0	5.48	2.25	2.16	1.59	1.59
09	1.52	2.16	2.16	1.92	2.00	25.6	11.5	5.48	2.16	1.92	1.67	1.59
10	1.52	2.16	2.16	1.75	1.92	18.3	12.3	5.48	2.16	1.75	1.84	1.59
11	1.52	2.16	2.16	1.75	2.00	14.8	12.0	4.90	2.33	1.75	1.67	1.59
12	1.59	2.16	2.16	1.84	2.16	14.0	11.3	4.71	2.25	1.75	1.67	1.59
13	1.44	2.16	2.16	1.75	2.16	15.5	10.8	4.52	2.25	1.75	1.67	1.59
14	1.44	2.16	2.16	1.75	2.08	18.5	10.8	4.52	2.25	1.75	1.67	1.59
15	1.44	2.33	2.08	1.67	2.08	17.0	10.2	4.52	2.16	1.75	1.67	1.59
16	1.44	2.41	2.16	1.52	1.84	14.5	9.96	4.33	2.16	1.75	1.67	1.59
17	1.44	2.25	2.25	1.59	1.75	12.8	9.42	5.29	2.25	1.67	1.67	1.59
18	1.44	2.25	2.25	1.59	2.00	12.3	8.60	5.29	3.10	1.67	1.67	1.59
19	1.44	2.25	2.53	1.67	2.00	12.5	8.06	4.71	2.76	1.67	1.67	1.59
20	1.52	2.41	2.99	1.67	1.92	10.5	7.56	4.33	2.41	1.67	1.67	1.59
21	1.59	2.33	2.76	1.59	2.00	9.96	7.33	4.14	2.33	1.59	1.67	1.59
22	1.39	2.33	2.53	1.52	2.00	10.2	7.33	3.94	2.25	1.59	1.67	1.75
23	1.39	2.33	2.53	1.67	2.00	10.5	7.79	3.75	2.16	1.59	1.67	1.75
24	1.39	2.33	2.53	1.75	2.08	11.5	8.06	3.56	2.08	1.59	1.67	1.84
25	1.39	2.33	2.25	1.75	2.08	19.5	10.8	3.45	2.08	1.59	1.59	1.59
26	1.39	2.33	2.00	1.75	2.25	17.5	8.33	3.10	2.00	1.52	1.59	1.59
27	1.39	2.33	2.00	1.75	2.53	15.3	7.79	3.56	2.08	1.52	1.59	1.52
28	1.39	2.25	1.92	1.59	2.87	14.5	7.33	3.45	2.33	1.52	1.59	1.52
29	1.39	2.25	2.00	1.67	-----	13.8	7.33	3.33	2.53	1.52	1.59	1.52
30	1.39	2.16	2.16	1.84	-----	13.3	7.10	3.22	2.25	1.52	1.59	1.52
31	1.39	-----	2.25	2.16	-----	14.3	-----	2.99	-----	1.67	1.59	-----
Maks.	1.84	2.87	3.22	2.41	2.99	38.4	17.5	7.56	3.33	2.33	2.00	2.16
Min.	1.31	1.84	1.75	1.52	1.44	2.99	6.87	2.87	1.92	1.52	1.52	1.44
Ortalama	1.49	2.23	2.24	1.80	1.98	14.5	10.2	4.74	2.31	1.78	1.64	1.60
LT/SN/Km2	1.97	2.96	2.97	2.39	2.62	19.3	13.5	6.28	3.07	2.36	2.17	2.12
AKIM mm.	5.29	7.67	7.95	6.41	6.35	51.6	35.0	16.8	7.95	6.32	5.81	5.50
MİL. M3	3.99	5.78	6.00	4.83	4.79	38.9	26.4	12.7	6.00	4.77	4.38	4.15

SU YILI (2006) YILLIK TOPLAM AKIM 122.69 MİLYON M3 163 MM. 5.2 LT/SN/Km2

18. Seyhan Havzasi

D18A034 DELİÇAY HOCALI

YERİ : **ADANA-ÇATALAN BARAJI SOL SAHİL YOLUNUN 15 KM SİNDEN SAĞA AYRILAN KÖY YOLUNUN 7. KM' SİNDEKİ HOCALI KÖYÜNDEDİR.**
35°25'15" Doğu - 37°8'59" Kuzey

YAĞIŞ ALANI : **35,40 km2** **YAKLAŞIK KOT : 115 m**

GÖZLEM SÜRESİ : **01.10.1990 - 30.09.2006**

ORTALAMA AKIMLAR : **Gözlem süresinde 0.159 m3/sn. (14 Yıllık) 2006 Su yılında 0.046 m3/sn.**

ANLIK EN ÇOK VE EN AZ AKIMLAR:

2006 Su yılında anlık ençok akım	:	**3.19**	**m3/sn**	**04.07.2006**
2006 Su yılında anlık enaz akım	:	**0.000**	**m3/sn**	**05.06.2006**
Gözlem süresinde anlık ençok akım	:	**110.**	**m3/sn**	**01.05.1994**
Gözlem süresinde anlık enaz akım	:	**0.000**	**m3/sn**	**16.06.1991**

Akımlar 01 Ekim 2005 'den 30 Eylül 2006' a kadar m3/sn olarak

Gün	Ekim	Kasım	Aralık	Ocak	Şubat	Mart	Nisan	Mayıs	Haziran	Temmuz	Ağustos	Eylül
01	0.011	0.040	0.063	0.040	0.021	0.080	0.066	0.066	0.025	0.034	KURU	KURU
02	0.011	0.040	0.063	0.040	0.021	0.066	0.066	0.066	0.025	0.025	KURU	KURU
03	0.011	0.040	0.063	0.040	0.021	0.052	0.066	0.080	0.025	0.025	KURU	KURU
04	0.011	0.040	0.063	0.040	0.021	0.052	0.052	0.052	0.034	0.480	KURU	KURU
05	0.011	0.040	0.063	0.040	0.040	0.052	0.052	0.034	0.010	0.080	KURU	KURU
06	0.011	0.040	0.063	0.040	0.040	0.052	0.052	0.034	KURU	0.066	KURU	KURU
07	0.011	0.040	0.063	0.040	0.040	0.052	0.052	0.034	KURU	0.052	KURU	KURU
08	0.011	0.040	0.063	0.040	0.524	0.066	0.052	0.025	KURU	0.043	KURU	KURU
09	0.011	0.021	0.063	0.040	0.142	0.066	0.052	0.034	KURU	0.034	KURU	KURU
10	0.011	0.021	0.063	0.103	0.063	0.126	0.043	0.052	KURU	0.034	KURU	KURU
11	0.011	0.021	0.063	0.021	0.063	0.126	0.043	0.043	KURU	0.025	KURU	KURU
12	0.011	0.021	0.063	0.040	0.142	0.126	0.043	0.043	KURU	0.017	KURU	KURU
13	0.011	0.021	0.063	0.021	0.063	0.126	0.043	0.034	KURU	0.010	KURU	KURU
14	0.011	0.021	0.063	0.040	0.040	0.100	0.034	0.034	KURU	KURU	KURU	KURU
15	0.011	0.021	0.063	0.063	0.040	0.100	0.034	0.043	KURU	KURU	KURU	KURU
16	0.011	0.021	0.063	0.040	0.040	0.100	0.034	0.043	KURU	KURU	KURU	KURU
17	0.011	0.021	0.063	0.021	0.021	0.100	0.034	0.034	KURU	KURU	KURU	KURU
18	0.021	0.021	0.142	0.063	0.021	0.126	0.034	0.043	KURU	KURU	KURU	KURU
19	0.103	0.021	1.75	0.103	0.021	0.126	0.034	0.066	KURU	KURU	KURU	KURU
20	0.186	0.021	0.298	0.103	0.021	0.126	0.034	0.052	KURU	KURU	KURU	KURU
21	0.186	0.063	0.142	0.063	0.021	0.126	0.034	0.034	KURU	KURU	KURU	KURU
22	0.186	0.063	0.103	0.063	0.021	0.126	0.034	0.034	KURU	KURU	KURU	KURU
23	0.186	0.063	0.103	0.063	0.021	0.126	0.034	0.034	KURU	KURU	KURU	KURU
24	0.186	0.063	0.063	0.040	0.080	0.126	0.034	0.034	KURU	KURU	KURU	KURU
25	0.142	0.063	0.040	0.040	0.080	0.080	0.034	0.034	KURU	KURU	KURU	0.034
26	0.103	0.063	0.040	0.040	0.080	0.066	0.034	0.025	KURU	KURU	KURU	0.043
27	0.063	0.063	0.040	0.021	0.066	0.066	0.025	0.017	KURU	KURU	KURU	0.025
28	0.040	0.063	0.040	0.021	0.066	0.066	0.034	0.025	KURU	KURU	KURU	0.025
29	0.040	0.063	0.040	0.021	-----	0.066	0.034	0.025	0.080	KURU	KURU	0.025
30	0.040	0.063	0.040	0.021	-----	0.066	0.034	0.025	0.043	0.010	KURU	0.025
31	0.040	-----	0.040	0.021	-----	0.066	-----	0.025	-----	0.010	KURU	-----
Maks.	0.186	0.063	2.23	0.443	1.31	0.214	0.100	0.080	0.126	3.19	0.010	0.043
Min.	0.011	0.021	0.040	0.011	0.011	0.043	0.017	0.010	KURU	KURU	KURU	KURU
Ortalama	0.055	0.040	0.127	0.045	0.066	0.090	0.042	0.039	0.008	0.030	KURU	0.006
LT/SN/Km2	1.56	1.13	3.60	1.27	1.86	2.55	1.18	1.12	0.228	0.861	0.000	0.167
AKIM mm.	4.17	2.93	9.65	3.40	4.49	6.83	3.05	2.99	0.591	2.31	0.000	0.432
MİL. M3	0.148	0.104	0.341	0.120	0.159	0.242	0.108	0.106	0.021	0.082	0.000	0.015

SU YILI (2006) YILLIK TOPLAM AKIM 1.45 MİLYON M3 41 MM. 1.3 LT/SN/Km2

18. Seyhan Havzasi

D18A036 GÖKSU N. FEKE

YERİ KÖPRÜSÜNDEDİR : **ADANA - TUFANBEYLİ YOLUNUN FEKE İLÇE MERKEZİNE 10 KM MESAFEDEKİ GÖKSU NEHRİ**

35°54'29" Doğu - 37°47'4" Kuzey

YAĞIŞ ALANI : **3456,90 km2** **YAKLAŞIK KOT : 495 m**

GÖZLEM SÜRESİ : **15.04.1993 - 30.09.2006**

ORTALAMA AKIMLAR : **Gözlem süresinde 44.069 m3/sn. (13 Yıllık) 2006 Su yılında 39.581 m3/sn.**

ANLIK EN ÇOK VE EN AZ AKIMLAR:

2006 Su yılında anlık ençok akım	**:**	**265.**	**m3/sn**	**09.03.2006**
2006 Su yılında anlık enaz akım	**:**	**15.2**	**m3/sn**	**03.10.2005**
Gözlem süresinde anlık ençok akım	**:**	**1308**	**m3/sn**	**20.11.1995**
Gözlem süresinde anlık enaz akım	**:**	**8.14**	**m3/sn**	**01.10.2001**

Akımlar 01 Ekim 2005 'den 30 Eylül 2006' a kadar m3/sn olarak

Gün	Ekim	Kasım	Aralık	Ocak	Şubat	Mart	Nisan	Mayıs	Haziran	Temmuz	Ağustos	Eylül
01	18.0	16.4	20.1	23.6	20.6	71.3	114.	55.1	31.8	28.6	18.5	15.8
02	18.0	17.4	19.6	23.6	20.6	79.0	126.	55.1	31.8	27.9	18.5	15.8
03	18.0	17.4	19.0	22.9	20.6	107.	124.	55.1	31.8	26.5	18.5	15.8
04	18.5	18.5	19.0	22.2	20.1	142.	108.	55.1	31.8	25.8	18.5	15.8
05	18.5	20.1	19.0	22.2	20.1	123.	99.8	55.1	31.8	25.8	18.5	15.8
06	17.4	19.6	18.5	22.2	23.6	112.	97.3	54.1	30.9	25.8	18.5	15.8
07	17.4	19.0	18.5	21.7	40.2	120.	97.3	52.2	30.9	25.0	18.5	15.8
08	17.4	18.5	18.5	21.7	63.9	145.	96.0	49.4	30.9	25.0	18.5	15.8
09	17.4	18.5	18.5	21.7	63.9	237.	98.5	50.4	30.1	24.3	18.5	15.8
10	17.4	18.5	18.5	21.7	61.9	160.	111.	49.4	29.3	24.3	18.5	15.8
11	16.9	18.5	18.5	21.7	79.0	127.	104.	48.5	29.3	23.6	18.5	15.8
12	16.9	18.0	18.5	21.1	94.8	114.	98.5	47.5	28.6	22.9	18.5	15.8
13	16.9	18.0	18.5	21.1	101.	102.	97.3	46.6	28.6	22.9	18.5	15.8
14	16.9	18.0	18.5	20.6	81.4	105.	94.8	46.6	27.9	22.9	18.5	15.8
15	16.9	18.0	18.5	20.6	68.0	114.	92.3	44.8	27.9	22.9	18.5	15.8
16	20.6	18.0	20.1	20.1	61.0	107.	89.8	43.9	27.9	22.9	18.5	15.8
17	22.2	18.0	21.1	20.1	56.0	105.	86.1	45.7	27.9	22.9	18.5	15.8
18	20.6	18.0	24.3	20.1	53.2	109.	79.0	45.7	27.9	22.9	19.6	15.8
19	19.6	18.0	111.	20.6	49.4	108.	74.5	43.9	27.2	22.9	18.5	15.8
20	18.5	18.5	82.6	22.9	45.7	98.5	70.2	43.0	27.2	22.9	17.4	15.8
21	18.5	25.8	57.0	21.7	44.8	94.8	69.1	41.1	27.2	21.7	16.4	15.8
22	18.5	28.6	44.8	20.6	45.7	86.1	68.0	40.2	27.2	20.6	16.4	15.8
23	18.0	24.3	35.9	20.1	48.5	84.9	67.0	40.2	27.2	20.6	16.4	15.8
24	18.0	21.7	34.2	20.1	48.5	96.0	65.9	40.2	26.5	20.6	16.4	16.4
25	18.0	21.1	33.4	21.1	48.5	160.	65.9	39.3	26.5	20.6	16.4	16.4
26	18.0	20.6	29.3	22.9	52.2	165.	63.9	38.4	26.5	20.6	16.4	16.9
27	18.0	20.6	26.5	24.3	61.0	135.	61.0	37.5	26.5	20.6	16.4	16.9
28	16.9	20.1	25.0	23.6	70.2	124.	58.0	36.7	26.5	19.6	15.8	16.9
29	15.8	20.1	25.0	22.9	-----	114.	57.0	35.9	29.3	19.6	15.8	16.4
30	15.8	20.1	25.0	21.7	-----	111.	56.0	34.2	30.1	19.0	15.8	16.4
31	16.9	-----	25.0	20.6	-----	112.	-----	32.6	-----	17.4	15.8	-----
Maks.	37.5	35.9	152.	25.0	105.	265.	129.	55.1	31.8	29.3	19.6	17.4
Min.	15.2	16.4	17.4	20.1	19.6	70.2	56.0	32.6	26.5	17.4	15.8	15.8
Ortalama	17.9	19.6	29.1	21.7	52.3	118.	86.3	45.3	28.8	22.9	17.7	16.0
LT/SN/Km2	5.19	5.67	8.42	6.27	15.1	34.2	25.0	13.1	8.34	6.62	5.11	4.63
AKIM mm.	13.9	14.7	22.5	16.8	36.6	91.7	64.7	35.1	21.6	17.7	13.7	12.0
MİL. M3	48.1	50.8	77.9	58.1	127.	317.	224.	121.	74.7	61.3	47.3	41.4

SU YILI (2006) YILLIK TOPLAM AKIM 1248.60 MİLYON M3 361 MM. 11.4 LT/SN/Km2

18. Seyhan Havzasi

D18A040 ÇÖRÜMŞEK DERESİ PANLI

YERİ : **KAYSERİ-MALATYA KARAYOLUNUN 75. KM SİNDE PANLI KÖYÜNDEDİR**
36°8'18" Doğu - 38°46'0" Kuzey

YAĞIŞ ALANI : **301,60 km2** **YAKLAŞIK KOT : 1493 m**

GÖZLEM SÜRESİ : **01.10.1995 - 30.09.2006**

ORTALAMA AKIMLAR : **Gözlem süresinde 0.136 m3/sn. (8 Yıllık) 2006 Su yılında 0.075 m3/sn.**

ANLIK EN ÇOK VE EN AZ AKIMLAR:

2006 Su yılında anlık ençok akım	**:**	**0.911 m3/sn**	**26.03.2006**
2006 Su yılında anlık enaz akım	**:**	**0.003 m3/sn**	**21.06.2006**
Gözlem süresinde anlık ençok akım	**:**	**2.93 m3/sn**	**04.04.2000**
Gözlem süresinde anlık enaz akım	**:**	**0.003 m3/sn**	**21.06.2006**

3. Anahtar Eğrisi (Seviyeler cm olarak)

Seviye	Akım	Seviye	Akım	Seviye	Akım	Seviye	Akım
1	0.000	6	0.017	11	0.074	41	1.1
2	0.000	7	0.025	16	0.165	51	1.7
3	0.003	8	0.036	21	0.295	61	2.4
4	0.007	9	0.047	26	0.449	71	3.2
5	0.011	10	0.061	31	0.652		

Akımlar 01 Ekim 2005 'den 30 Eylül 2006' a kadar m3/sn olarak

Gün	Ekim	Kasım	Aralık	Ocak	Şubat	Mart	Nisan	Mayıs	Haziran	Temmuz	Ağustos	Eylül
01	0.025	0.036	0.071	0.091	0.198	0.198	0.153	0.091	0.047	0.074	0.011	0.017
02	0.025	0.036	0.071	0.091	0.198	0.198	0.153	0.092	0.047	0.036	0.007	0.017
03	0.025	0.036	0.071	0.109	0.198	0.198	0.249	0.165	0.036	0.036	0.011	0.017
04	0.025	0.036	0.071	0.131	0.220	0.220	0.176	0.243	0.036	0.036	0.011	0.017
05	0.025	0.036	0.071	0.153	0.176	0.176	0.153	0.147	0.036	0.036	0.011	0.017
06	0.025	0.071	0.071	0.153	0.153	0.153	0.153	0.110	0.036	0.036	0.011	0.017
07	0.025	0.071	0.071	0.131	0.153	0.153	0.131	0.110	0.025	0.036	0.011	0.017
08	0.025	0.071	0.071	0.109	0.131	0.153	0.131	0.110	0.025	0.025	0.007	0.017
09	0.025	0.071	0.091	0.131	0.131	0.131	0.131	0.110	0.025	0.025	0.011	0.017
10	0.025	0.071	0.091	0.109	0.131	0.131	0.109	0.110	0.025	0.017	0.011	0.017
11	0.025	0.071	0.091	0.091	0.131	0.131	0.091	0.092	0.036	0.017	0.011	0.017
12	0.025	0.071	0.091	0.109	0.131	0.131	0.109	0.074	0.025	0.011	0.011	0.017
13	0.036	0.071	0.091	0.109	0.109	0.109	0.109	0.074	0.017	0.017	0.007	0.017
14	0.036	0.071	0.091	0.109	0.109	0.109	0.109	0.074	0.017	0.017	0.007	0.017
15	0.036	0.071	0.091	0.109	0.109	0.109	0.109	0.074	0.017	0.011	0.003	0.017
16	0.036	0.071	0.091	0.109	0.109	0.109	0.109	0.074	0.017	0.011	0.011	0.017
17	0.036	0.071	0.091	0.109	0.109	0.109	0.109	0.074	0.011	0.011	0.011	0.017
18	0.036	0.071	0.091	0.131	0.109	0.109	0.091	0.092	0.011	0.011	0.011	0.017
19	0.036	0.071	0.091	0.131	0.131	0.131	0.091	0.074	0.011	0.011	0.011	0.017
20	0.036	0.071	0.091	0.131	0.091	0.153	0.091	0.074	0.007	0.011	0.011	0.017
21	0.036	0.071	0.091	0.153	0.091	0.176	0.091	0.074	0.007	0.011	0.011	0.017
22	0.036	0.071	0.091	0.153	0.091	0.220	0.091	0.061	0.007	0.011	0.011	0.017
23	0.036	0.091	0.091	0.176	0.091	0.176	0.091	0.047	0.011	0.007	0.007	0.017
24	0.036	0.091	0.091	0.176	0.091	0.153	0.091	0.061	0.047	0.011	0.011	0.017
25	0.036	0.071	0.091	0.198	0.109	0.249	0.091	0.047	0.061	0.011	0.011	0.017
26	0.036	0.071	0.091	0.198	0.109	0.497	0.091	0.047	0.036	0.011	0.011	0.017
27	0.036	0.071	0.091	0.198	0.131	0.249	0.091	0.061	0.025	0.011	0.011	0.017
28	0.036	0.071	0.091	0.198	0.153	0.198	0.091	0.061	0.017	0.007	0.017	0.017
29	0.036	0.071	0.091	0.198	-----	0.176	0.091	0.061	0.017	0.007	0.017	0.017
30	0.036	0.071	0.091	0.198	-----	0.176	0.091	0.047	0.036	0.003	0.017	0.017
31	0.036	-----	0.091	0.198	-----	0.153	-----	0.047	-----	0.007	0.017	-----
Maks.	0.036	0.091	0.153	0.308	0.220	0.911	0.308	0.418	0.418	0.326	0.025	0.074
Min.	0.025	0.036	0.055	0.071	0.026	0.091	0.071	0.036	0.003	0.003	0.003	0.017
Ortalama	0.032	0.066	0.086	0.142	0.132	0.172	0.116	0.086	0.026	0.019	0.011	0.017
LT/SN/Km2	0.105	0.220	0.285	0.470	0.437	0.571	0.383	0.286	0.085	0.062	0.036	0.056
AKIM mm.	0.282	0.572	0.762	1.26	1.06	1.53	0.993	0.767	0.221	0.167	0.097	0.146
MİL. M3	0.085	0.172	0.230	0.379	0.319	0.461	0.300	0.231	0.067	0.050	0.029	0.044

SU YILI (2006) YILLIK TOPLAM AKIM 2.37 MİLYON M3 8 MM. 0.2 LT/SN/Km2

18. Seyhan Havzasi

D18A042 HACİBİLİK ÇEŞMESİ ÇERKEZSÖĞÜT

YERİ İNLİÖREN : KAYSERİ SARIOĞLAN MALATYA YOLUNUN EKREK KÖYÜNDEN SOLA GİRVE-Lİ-HASSA-TOZGÜN-Ç.SÖĞÜTLÜ-KÖYÜNÜN İÇİNDEN KUZEYE TAŞLIHÖYÜK MEVKİİ YOLUNA GİRİLİR.KÖYE 1 KM MESAFEDEDİR. 36°16'0" Doğu - 38°50'30" Kuzey

YAĞIŞ ALANI : 68,00 km2 **YAKLAŞIK KOT :** 1615 m

GÖZLEM SÜRESİ : 01.10.1997 - 30.09.2006

ORTALAMA AKIMLAR : Gözlem süresinde 0.028 m3/sn. (6 Yıllık) 2006 Su yılında 0.014 m3/sn.

ANLIK EN ÇOK VE EN AZ AKIMLAR:

2006 Su yılında anlık ençok akım	:	0.345 m3/sn	24.05.2006
2006 Su yılında anlık enaz akım	:	0.000 m3/sn	01.10.2005
Gözlem süresinde anlık ençok akım	:	0.633 m3/sn	01.03.2005
Gözlem süresinde anlık enaz akım	:	0.000 m3/sn	01.10.2001

2. Anahtar Eğrisi (Seviyeler cm olarak)

Seviye	Akım	Seviye	Akım	Seviye	Akım
1	0.000	7	0.035	51	0.851
2	0.001	13	0.120	61	1.0
3	0.004	19	0.234	65	1.1
4	0.010	37	0.568		
5	0.018	41	0.654		

Akımlar 01 Ekim 2005 'den 30 Eylül 2006' a kadar m3/sn olarak

Gün	Ekim	Kasım	Aralık	Ocak	Şubat	Mart	Nisan	Mayıs	Haziran	Temmuz	Ağustos	Eylül
01	KURU	KURU	KURU	KURU	KURU	0.049	0.035	0.018	KURU	KURU	KURU	KURU
02	KURU	KURU	KURU	KURU	KURU	0.049	0.063	0.035	KURU	KURU	KURU	KURU
03	KURU	KURU	KURU	KURU	KURU	0.049	0.078	0.018	KURU	KURU	KURU	KURU
04	KURU	KURU	KURU	KURU	KURU	0.063	0.004	0.106	KURU	KURU	KURU	KURU
05	KURU	KURU	KURU	KURU	KURU	0.035	0.035	0.290	KURU	KURU	KURU	KURU
06	KURU	KURU	KURU	KURU	KURU	0.049	0.035	0.290	KURU	KURU	KURU	KURU
07	KURU	KURU	KURU	KURU	KURU	0.049	0.035	0.234	KURU	KURU	KURU	KURU
08	KURU	KURU	KURU	KURU	KURU	0.049	0.035	0.177	KURU	KURU	KURU	KURU
09	KURU	KURU	KURU	KURU	KURU	0.035	0.035	0.106	KURU	KURU	KURU	KURU
10	KURU	KURU	KURU	KURU	KURU	0.035	0.035	0.092	KURU	KURU	KURU	KURU
11	KURU	KURU	KURU	KURU	KURU	0.035	0.035	0.078	KURU	KURU	KURU	KURU
12	KURU	KURU	KURU	KURU	KURU	0.035	0.035	0.078	KURU	KURU	KURU	KURU
13	KURU	KURU	KURU	KURU	KURU	0.035	0.035	0.078	KURU	KURU	KURU	KURU
14	KURU	KURU	KURU	KURU	KURU	0.035	0.035	0.063	KURU	KURU	KURU	KURU
15	KURU	KURU	KURU	KURU	KURU	0.035	0.035	0.063	KURU	KURU	KURU	KURU
16	KURU	KURU	KURU	KURU	KURU	0.035	0.035	0.063	KURU	KURU	KURU	KURU
17	KURU	KURU	KURU	KURU	KURU	0.035	0.027	0.063	KURU	KURU	KURU	KURU
18	KURU	KURU	KURU	KURU	KURU	0.035	0.027	0.063	KURU	KURU	KURU	KURU
19	KURU	KURU	KURU	KURU	KURU	0.035	0.010	0.063	KURU	KURU	KURU	KURU
20	KURU	KURU	KURU	KURU	KURU	0.035	0.010	0.063	KURU	KURU	KURU	KURU
21	KURU	KURU	KURU	KURU	KURU	0.035	0.010	0.063	KURU	KURU	KURU	KURU
22	KURU	KURU	KURU	KURU	KURU	0.035	0.010	0.063	KURU	KURU	KURU	KURU
23	KURU	KURU	KURU	KURU	KURU	0.049	0.010	0.063	KURU	KURU	KURU	KURU
24	KURU	KURU	KURU	KURU	KURU	0.049	0.010	0.177	KURU	KURU	KURU	KURU
25	KURU	KURU	KURU	KURU	KURU	0.106	0.018	0.139	KURU	KURU	KURU	KURU
26	KURU	KURU	KURU	KURU	KURU	0.158	0.027	0.063	KURU	KURU	KURU	KURU
27	KURU	KURU	KURU	KURU	KURU	0.158	0.027	0.049	KURU	KURU	KURU	KURU
28	KURU	KURU	KURU	KURU	KURU	0.158	0.018	0.027	KURU	KURU	KURU	KURU
29	KURU	KURU	KURU	KURU	-----	0.078	0.018	0.018	KURU	KURU	KURU	KURU
30	KURU	KURU	KURU	KURU	-----	0.035	0.018	0.010	KURU	KURU	KURU	KURU
31	KURU	-----	KURU	KURU	-----	0.035	-----	KURU	-----	KURU	KURU	-----
Maks.	KURU	KURU	KURU	KURU	KURU	0.234	0.106	0.345	KURU	KURU	KURU	KURU
Min.	KURU	KURU	KURU	KURU	KURU	KURU	KURU	KURU	KURU	KURU	KURU	KURU
Ortalama	KURU	KURU	KURU	KURU	KURU	0.055	0.028	0.088	KURU	KURU	KURU	KURU
LT/SN/Km2	0.000	0.000	0.000	0.000	0.000	0.810	0.412	1.29	0.000	0.000	0.000	0.000
AKIM mm.	0.000	0.000	0.000	0.000	0.000	2.17	1.07	3.45	0.000	0.000	0.000	0.000
MİL. M3	0.000	0.000	0.000	0.000	0.000	0.148	0.073	0.234	0.000	0.000	0.000	0.000

SU YILI (2006) YILLIK TOPLAM AKIM 0.45 MİLYON M3 7 MM. 0.2 LT/SN/Km2

18. Seyhan Havzasi

D18A047 ZAMANTI IRMAĞI ÇAMLICA HES

YERİ : **YENİ AÇILAN YAHYALI-ADANA YOLUNUN 20.KM SINDEN SOLA ŞIHLI-KARAKÖY YOLUNA GIRILIR 1KM ILERIDE MALZEME OCAĞININ MEMBASINDA KAYALARIN BAŞLANGICINDA,HES.REGÜLATÖRÜNÜN 2KM.MEMBASINDADIR.**

35°31'14" Doğu - 38°1'50" Kuzey

YAĞIŞ ALANI : **7184.10 km2** **YAKLAŞIK KOT : 1185 m**

GÖZLEM SÜRESİ : **01.10.1998 - 30.09.2006**

ORTALAMA AKIMLAR : **Gözlem süresinde 10.914 m3/sn. (3 Yıllık) 2006 Su yılında 10.914 m3/sn.**

ANLIK EN ÇOK VE EN AZ AKIMLAR:

2006 Su yılında anlık ençok akım	**:**	**34.4**	**m3/sn**	**25.04.2006**
2006 Su yılında anlık enaz akım	**:**	**2.35**	**m3/sn**	**17.02.2006**
Gözlem süresinde anlık ençok akım	**:**	**81.3**	**m3/sn**	**07.03.2004**
Gözlem süresinde anlık enaz akım	**:**	**2.35**	**m3/sn**	**17.02.2006**

4. Anahtar Eğrisi (Seviyeler cm olarak)

Seviye	Akım	Seviye	Akım	Seviye	Akım	Seviye	Akım
54	2.2	90	13.0	140	38.9	190	76.0
56	2.5	100	17.3	150	46.3	200	83.5
60	3.4	110	22.1	160	53.7		
70	6.0	120	27.0	170	61.1		
80	9.0	130	32.3	180	68.5		

Akımlar 01 Ekim 2005 'den 30 Eylül 2006' a kadar m3/sn olarak

Gün	Ekim	Kasım	Aralık	Ocak	Şubat	Mart	Nisan	Mayıs	Haziran	Temmuz	Ağustos	Eylül
01	5.48	5.48	5.22	11.0	5.48	5.74	25.1	27.2	8.10	11.2	7.10	7.32
02	5.48	5.48	5.48	9.00	6.00	6.00	28.8	28.3	9.00	10.5	6.88	7.32
03	5.48	5.48	6.30	8.70	6.30	6.60	26.7	29.3	9.40	9.67	6.88	6.88
04	6.30	5.48	7.80	8.10	8.70	8.40	21.2	27.7	9.80	9.11	6.88	6.88
05	6.60	5.48	8.70	7.80	8.40	8.10	18.5	28.3	9.40	8.83	6.88	6.88
06	6.00	5.48	9.40	6.30	9.80	7.80	17.4	29.3	10.6	9.67	6.65	6.88
07	5.74	5.48	11.4	6.00	9.40	11.4	17.0	29.3	9.40	10.8	6.43	6.88
08	5.74	5.48	11.8	5.74	6.90	14.3	17.7	29.3	9.80	10.2	6.21	6.65
09	5.74	4.96	12.2	5.74	10.6	16.4	20.3	30.4	9.40	9.95	6.43	6.88
10	5.74	4.18	12.2	6.00	10.2	15.2	25.7	29.9	8.40	10.8	6.43	7.10
11	5.74	3.66	12.2	8.40	8.10	12.2	28.3	29.3	8.40	9.39	6.65	7.32
12	5.74	3.66	12.2	14.3	5.74	10.6	26.2	29.3	9.40	8.54	6.65	7.32
13	5.74	3.66	12.2	15.2	5.48	9.40	26.2	29.9	9.40	8.83	6.88	7.54
14	5.48	3.66	12.2	15.2	5.22	9.80	31.0	29.9	9.40	8.26	6.65	7.54
15	5.48	3.66	12.2	15.2	4.96	11.0	30.4	27.2	8.70	8.26	6.65	7.76
16	5.74	3.66	12.6	12.2	4.44	11.0	31.0	27.7	8.10	8.54	7.54	7.54
17	6.30	3.66	11.4	6.90	3.92	10.6	31.6	24.1	7.80	8.26	7.76	7.98
18	6.30	3.66	10.6	5.74	3.66	9.00	30.4	22.8	7.50	7.98	7.98	7.98
19	6.30	3.66	14.3	5.74	3.92	9.40	28.8	25.7	6.90	7.98	7.98	8.26
20	6.00	3.66	14.7	6.90	3.92	13.0	27.7	23.3	6.90	7.76	7.54	7.98
21	6.00	3.66	14.7	6.60	3.92	12.2	28.8	21.6	6.60	7.76	7.32	8.26
22	6.00	4.44	13.9	7.20	3.92	11.8	27.7	21.2	6.00	7.76	7.32	8.54
23	6.00	4.44	12.6	7.50	3.92	13.9	27.7	21.2	5.48	7.98	7.32	9.11
24	6.00	3.92	9.40	8.40	4.18	16.4	27.7	20.7	5.22	7.98	6.88	9.39
25	6.00	3.66	10.6	8.10	4.18	25.1	31.6	14.3	5.48	7.76	6.65	9.11
26	6.00	3.92	9.80	7.80	4.70	29.3	31.0	13.0	5.22	7.54	6.88	9.11
27	7.20	3.92	7.50	7.80	5.48	26.7	27.2	12.2	5.48	6.65	7.10	9.67
28	6.90	3.92	8.10	7.20	6.00	24.1	25.7	11.8	5.74	7.54	7.32	10.5
29	6.90	4.18	8.10	5.48	-----	23.3	25.1	11.0	6.90	7.54	7.10	10.8
30	5.48	4.70	12.2	4.96	-----	23.3	24.6	9.00	11.2	7.54	7.32	10.8
31	5.48	-----	9.80	4.96	-----	24.1	-----	8.40	-----	7.10	7.54	-----
Maks.	8.40	5.48	19.7	15.6	11.0	33.3	34.4	31.6	11.2	11.9	8.83	11.9
Min.	5.48	3.66	5.22	4.44	2.35	5.74	16.7	7.80	4.70	5.99	5.99	6.43
Ortalama	5.97	4.34	10.7	8.26	5.98	14.1	26.2	23.3	7.97	8.63	7.03	8.07
LT/SN/Km2	0.831	0.605	1.49	1.15	0.832	1.96	3.65	3.24	1.11	1.20	0.978	1.12
AKIM mm.	2.23	1.57	3.99	3.08	2.01	5.25	9.47	8.69	2.88	3.22	2.62	2.91
MİL. M3	16.0	11.3	28.7	22.1	14.5	37.7	68.0	62.4	20.7	23.1	18.8	20.9

SU YILI (2006) YILLIK TOPLAM AKIM 344.20 MİLYON M3 48 MM. 1.5 LT/SN/Km2

18. Seyhan Havzasi

D18A048 TOTARİ DERESİ BADEMDERE

YERİ : KAYSERI-CAMARDI-BADEMDERE YOLUNDAN PINARBASI KOYUNE DONULUR.PINARBASINA VARILMADAN TOTARI DERESININ 2 KM MENBASINDADIR.
35°7'1" Doğu - 37°54'27" Kuzey

YAĞIŞ ALANI : 64,34 km2 **YAKLAŞIK KOT :** 1613,31 m

GÖZLEM SÜRESİ : 01.10.2003 - 30.09.2006

ORTALAMA AKIMLAR : Gözlem süresinde 0.719 m3/sn. (3 Yıllık) 2006 Su yılında 0.399 m3/sn.

ANLIK EN ÇOK VE EN AZ AKIMLAR:

2006 Su yılında anlık ençok akım	:	2.29	m3/sn	24.05.2006
2006 Su yılında anlık enaz akım	:	0.001	m3/sn	08.03.2006
Gözlem süresinde anlık ençok akım	:	6.34	m3/sn	23.05.2005
Gözlem süresinde anlık enaz akım	:	0.001	m3/sn	18.10.2004

2. Anahtar Eğrisi (Seviyeler cm olarak)

Seviye	Akım	Seviye	Akım	Seviye	Akım
1	0.000	7	0.210	21	1.9
2	0.001	8	0.290	26	3.0
3	0.009	9	0.360	31	4.6
4	0.042	11	0.560	41	7.5
5	0.086	16	1.1		

Akımlar 01 Ekim 2005 'den 30 Eylül 2006' a kadar m3/sn olarak

Gün	Ekim	Kasım	Aralık	Ocak	Şubat	Mart	Nisan	Mayıs	Haziran	Temmuz	Ağustos	Eylül
01	0.045	0.045	0.045	0.045	0.180	0.280	0.001	1.36	1.76	0.668	0.360	0.086
02	0.045	0.045	0.045	0.045	0.180	0.280	0.009	1.63	1.76	0.668	0.210	0.086
03	0.045	0.045	0.045	0.045	0.180	0.280	0.086	1.50	1.63	0.560	0.086	0.042
04	0.045	0.045	0.045	0.045	0.180	0.280	0.148	1.50	1.50	0.560	0.086	0.042
05	0.045	0.045	0.045	0.045	0.180	0.280	0.210	1.50	1.50	0.560	0.086	0.042
06	0.045	0.045	0.045	0.045	0.180	0.280	0.290	1.50	1.36	0.560	0.086	0.042
07	0.045	0.045	0.045	0.045	0.180	0.280	0.290	1.50	1.36	0.460	0.086	0.042
08	0.045	0.045	0.045	0.045	0.180	0.009	0.290	1.76	1.23	0.460	0.086	0.042
09	0.045	0.045	0.045	0.045	0.180	0.001	0.290	1.87	1.23	0.460	0.086	0.042
10	0.045	0.045	0.045	0.045	0.180	0.001	0.460	1.76	0.992	0.460	0.086	0.042
11	0.045	0.045	0.045	0.045	0.180	0.042	0.560	1.76	0.992	0.360	0.086	0.042
12	0.045	0.045	0.045	0.045	0.180	0.009	0.560	1.87	0.884	0.360	0.086	0.042
13	0.045	0.045	0.045	0.045	0.180	0.001	0.776	1.97	0.776	0.360	0.086	0.042
14	0.045	0.045	0.045	0.280	0.180	0.001	0.884	1.97	0.668	0.360	0.086	0.042
15	0.045	0.045	0.045	0.280	0.180	0.001	0.884	1.97	0.668	0.360	0.086	0.042
16	0.045	0.045	0.045	0.180	0.180	0.001	1.23	1.97	0.668	0.360	0.086	0.042
17	0.045	0.045	0.045	0.180	0.180	0.001	1.76	1.97	0.668	0.360	0.086	0.042
18	0.045	0.045	0.045	0.180	0.180	0.001	1.76	1.87	0.668	0.360	0.148	0.042
19	0.045	0.045	0.045	0.180	0.180	0.001	1.50	1.76	0.560	0.360	0.290	0.042
20	0.045	0.045	0.045	0.180	0.280	0.001	1.50	1.76	0.460	0.360	0.210	0.042
21	0.045	0.045	0.045	0.180	0.280	0.001	1.87	1.87	0.460	0.360	0.210	0.042
22	0.045	0.045	0.045	0.180	0.280	0.001	1.87	1.87	0.460	0.360	0.210	0.042
23	0.045	0.045	0.045	0.180	0.280	0.001	1.76	1.97	0.460	0.360	0.210	0.042
24	0.045	0.045	0.045	0.180	0.180	0.001	1.76	2.29	0.290	0.360	0.210	0.042
25	0.045	0.045	0.045	0.180	0.180	0.001	1.63	2.29	0.360	0.360	0.148	0.042
26	0.045	0.045	0.045	0.180	0.180	0.001	1.36	2.18	0.290	0.360	0.148	0.042
27	0.045	0.045	0.045	0.180	0.180	0.001	1.23	2.18	0.290	0.360	0.148	0.042
28	0.045	0.045	0.045	0.180	0.280	0.001	1.10	2.08	0.290	0.360	0.148	0.042
29	0.045	0.045	0.045	0.180	-----	0.001	0.992	2.08	0.290	0.360	0.148	0.042
30	0.045	0.045	0.045	0.180	-----	0.001	1.10	2.08	0.776	0.360	0.148	0.042
31	0.045	-----	0.045	0.180	-----	0.001	-----	1.97	-----	0.360	0.148	-----
Maks.	0.045	0.045	0.045	0.380	0.380	0.490	1.97	2.29	1.87	0.668	0.460	0.148
Min.	0.045	0.045	0.045	0.045	0.180	0.001	0.001	1.10	0.210	0.360	0.042	0.042
Ortalama	0.045	0.045	0.045	0.130	0.198	0.066	0.939	1.86	0.843	0.419	0.141	0.045
LT/SN/Km2	0.699	0.699	0.699	2.02	3.08	1.02	14.6	28.9	13.1	6.51	2.20	0.698
AKIM mm.	1.87	1.81	1.87	5.41	7.44	2.74	37.8	77.4	34.0	17.4	5.89	1.81
MİL. M3	0.121	0.117	0.121	0.348	0.479	0.176	2.43	4.98	2.19	1.12	0.379	0.116

SU YILI (2006) YILLIK TOPLAM AKIM 12.58 MİLYON M3 195 MM. 6.2 LT/SN/Km2

18. Seyhan Havzasi

D18A049 EGNELLİÖZÜ DERESI EGNELLİ

YERİ : KAYSERI CAMARDI YOLUNUN 130 KM SINDEN EYNELLI KOYUNE DONULURISTASYON KOYUN ICERISINDE SAGLIK OCAGI KARSISINDADIR.
35°0'48" Doğu - 37°55'53" Kuzey

YAĞIŞ ALANI : 18,02 km2 **YAKLAŞIK KOT :** 1636 m

GÖZLEM SÜRESİ : 01.10.2003 - 30.09.2006

ORTALAMA AKIMLAR : Gözlem süresinde 0.168 m3/sn. (3 Yıllık) 2006 Su yılında 0.109 m3/sn.

ANLIK EN ÇOK VE EN AZ AKIMLAR:

2006 Su yılında anlık ençok akım	:	0.262 m3/sn	09.05.2006
2006 Su yılında anlık enaz akım	:	0.062 m3/sn	01.10.2005
Gözlem süresinde anlık ençok akım	:	1.50 m3/sn	21.06.2004
Gözlem süresinde anlık enaz akım	:	0.062 m3/sn	01.10.2003

1. Anahtar Eğrisi (Seviyeler cm olarak)

Seviye	Akım	Seviye	Akım	Seviye	Akım
1	0.000	6	0.010	26	0.830
2	0.000	8	0.038	31	1.2
3	0.001	11	0.110	71	3.5
4	0.002	16	0.300		
5	0.006	21	0.530		

Akımlar 01 Ekim 2005 'den 30 Eylül 2006' a kadar m3/sn olarak

Gün	Ekim	Kasım	Aralık	Ocak	Şubat	Mart	Nisan	Mayıs	Haziran	Temmuz	Ağustos	Eylül
01	0.062	0.062	0.110	0.086	0.086	0.110	0.110	0.186	0.148	0.110	0.110	0.086
02	0.062	0.062	0.110	0.086	0.086	0.110	0.186	0.186	0.148	0.110	0.062	0.110
03	0.062	0.062	0.110	0.086	0.086	0.110	0.224	0.186	0.148	0.110	0.062	0.110
04	0.062	0.086	0.110	0.086	0.086	0.110	0.224	0.224	0.148	0.110	0.086	0.110
05	0.062	0.086	0.110	0.086	0.086	0.110	0.186	0.224	0.148	0.110	0.086	0.110
06	0.062	0.086	0.086	0.086	0.086	0.110	0.148	0.224	0.148	0.110	0.086	0.110
07	0.062	0.086	0.086	0.086	0.086	0.110	0.148	0.224	0.148	0.186	0.086	0.110
08	0.062	0.086	0.086	0.086	0.086	0.110	0.148	0.224	0.148	0.148	0.086	0.110
09	0.062	0.086	0.086	0.086	0.086	0.110	0.148	0.224	0.110	0.110	0.086	0.110
10	0.062	0.086	0.086	0.086	0.086	0.110	0.148	0.186	0.110	0.110	0.086	0.110
11	0.062	0.086	0.086	0.086	0.086	0.110	0.148	0.186	0.110	0.110	0.086	0.110
12	0.062	0.086	0.086	0.086	0.086	0.110	0.148	0.186	0.110	0.110	0.086	0.110
13	0.062	0.086	0.086	0.086	0.086	0.110	0.148	0.186	0.110	0.110	0.086	0.110
14	0.062	0.086	0.086	0.086	0.086	0.110	0.148	0.186	0.110	0.110	0.086	0.110
15	0.062	0.086	0.086	0.086	0.086	0.110	0.148	0.186	0.110	0.110	0.086	0.110
16	0.062	0.110	0.086	0.086	0.086	0.110	0.148	0.186	0.110	0.110	0.086	0.110
17	0.062	0.110	0.086	0.086	0.086	0.110	0.148	0.186	0.110	0.110	0.086	0.110
18	0.062	0.110	0.086	0.086	0.086	0.110	0.148	0.186	0.086	0.110	0.086	0.110
19	0.062	0.110	0.086	0.086	0.086	0.110	0.148	0.186	0.086	0.110	0.086	0.110
20	0.062	0.110	0.086	0.086	0.086	0.110	0.148	0.186	0.086	0.110	0.086	0.110
21	0.062	0.110	0.086	0.086	0.086	0.110	0.148	0.186	0.086	0.110	0.086	0.110
22	0.062	0.110	0.086	0.086	0.086	0.110	0.148	0.186	0.086	0.110	0.086	0.110
23	0.062	0.110	0.086	0.086	0.110	0.110	0.186	0.186	0.086	0.110	0.086	0.110
24	0.062	0.110	0.086	0.086	0.110	0.110	0.186	0.148	0.086	0.110	0.086	0.110
25	0.062	0.110	0.086	0.086	0.110	0.110	0.224	0.148	0.086	0.110	0.086	0.110
26	0.062	0.110	0.086	0.086	0.110	0.110	0.224	0.148	0.086	0.110	0.086	0.110
27	0.062	0.110	0.086	0.086	0.110	0.110	0.224	0.148	0.086	0.110	0.086	0.110
28	0.062	0.110	0.086	0.086	0.110	0.110	0.186	0.148	0.086	0.110	0.086	0.110
29	0.062	0.110	0.086	0.086	-----	0.110	0.186	0.148	0.086	0.110	0.086	0.110
30	0.062	0.110	0.086	0.086	-----	0.110	0.186	0.148	0.110	0.110	0.086	0.110
31	0.062	-----	0.086	0.086	-----	0.110	-----	0.148	-----	0.110	0.086	-----
Maks.	0.062	0.110	0.148	0.086	0.110	0.110	0.224	0.262	0.186	0.224	0.110	0.110
Min.	0.062	0.062	0.062	0.086	0.086	0.110	0.110	0.148	0.086	0.110	0.062	0.086
Ortalama	0.062	0.096	0.090	0.086	0.091	0.110	0.168	0.184	0.111	0.114	0.085	0.109
LT/SN/Km2	3.44	5.31	4.99	4.77	5.06	6.10	9.34	10.2	6.13	6.31	4.73	6.06
AKIM mm.	9.22	13.8	13.4	12.8	12.2	16.3	24.2	27.3	15.9	16.9	12.7	15.7
MİL. M3	0.166	0.248	0.241	0.230	0.220	0.295	0.436	0.492	0.287	0.304	0.228	0.283

SU YILI (2006) YILLIK TOPLAM AKIM 3.43 MİLYON M3 190 MM. 6.0 LT/SN/Km2

18. Seyhan Havzasi

D18A050 HAMACA DERESİ BADEMDERE

YERİ : **KAYSERİ -ÇAMARDI KARAYOLUNUN 120.KM SINDE BADEMDERE BELDESINE 3 KM KALA YOLUN SAĞINDADIR HER MEVSIM ULAŞIM SAĞLANIR.**
35°4'52" Doğu - 37°56'17" Kuzey

YAĞIŞ ALANI : **26,50 km2** **YAKLAŞIK KOT : 1608 m**

GÖZLEM SÜRESİ : **01.10.2003 - 30.09.2006**

ORTALAMA AKIMLAR : **Gözlem süresinde 0.027 m3/sn. (3 Yıllık) 2006 Su yılında 0.018 m3/sn.**

ANLIK EN ÇOK VE EN AZ AKIMLAR:

2006 Su yılında anlık ençok akım	**:**	**0.361 m3/sn**	**03.05.2006**
2006 Su yılında anlık enaz akım	**:**	**0.000 m3/sn**	**01.10.2005**
Gözlem süresinde anlık ençok akım	**:**	**2.93 m3/sn**	**04.04.2000**
Gözlem süresinde anlık enaz akım	**:**	**0.000 m3/sn**	**01.10.2003**

2. Anahtar Eğrisi (Seviyeler cm olarak)

Seviye	Akım	Seviye	Akım
1	0.012	10	0.400
2	0.045	20	0.865
3	0.080	30	1.4
4	0.120		
5	0.166		

Akımlar 01 Ekim 2005 'den 30 Eylül 2006' a kadar m3/sn olarak

Gün	Ekim	Kasım	Aralık	Ocak	Şubat	Mart	Nisan	Mayıs	Haziran	Temmuz	Ağustos	Eylül
01	KURU	KURU	KURU	KURU	KURU	KURU	0.022	0.213	KURU	KURU	KURU	KURU
02	KURU	KURU	KURU	KURU	KURU	KURU	0.022	0.213	KURU	KURU	KURU	KURU
03	KURU	KURU	KURU	KURU	KURU	KURU	0.022	0.263	KURU	KURU	KURU	KURU
04	KURU	KURU	KURU	KURU	KURU	KURU	0.022	0.263	KURU	KURU	KURU	KURU
05	KURU	KURU	KURU	KURU	KURU	KURU	0.065	0.022	KURU	KURU	KURU	KURU
06	KURU	KURU	KURU	KURU	KURU	KURU	0.164	0.263	KURU	KURU	KURU	KURU
07	KURU	KURU	KURU	KURU	KURU	KURU	0.114	0.213	KURU	KURU	KURU	KURU
08	KURU	KURU	KURU	KURU	KURU	KURU	0.065	0.213	KURU	KURU	KURU	KURU
09	KURU	KURU	KURU	KURU	KURU	KURU	0.065	0.164	KURU	KURU	KURU	KURU
10	KURU	KURU	KURU	KURU	KURU	KURU	0.065	0.065	KURU	KURU	KURU	KURU
11	KURU	KURU	KURU	KURU	KURU	KURU	0.065	0.022	KURU	KURU	KURU	KURU
12	KURU	KURU	KURU	KURU	KURU	KURU	0.114	0.022	KURU	KURU	KURU	KURU
13	KURU	KURU	KURU	KURU	KURU	KURU	0.114	0.022	KURU	KURU	KURU	KURU
14	KURU	KURU	KURU	KURU	KURU	KURU	0.114	0.120	0.012	KURU	KURU	KURU
15	KURU	KURU	KURU	KURU	KURU	KURU	0.114	0.120	0.012	KURU	KURU	KURU
16	KURU	KURU	KURU	KURU	KURU	0.022	0.114	0.080	0.012	KURU	KURU	KURU
17	KURU	KURU	KURU	KURU	KURU	0.022	0.114	0.045	0.012	KURU	KURU	KURU
18	KURU	KURU	KURU	KURU	KURU	0.022	0.114	KURU	0.012	KURU	KURU	KURU
19	KURU	KURU	KURU	KURU	KURU	0.022	0.114	KURU	0.012	KURU	KURU	KURU
20	KURU	KURU	KURU	KURU	KURU	0.022	0.114	KURU	0.012	KURU	KURU	KURU
21	KURU	KURU	KURU	KURU	KURU	0.022	0.114	KURU	0.012	KURU	KURU	KURU
22	KURU	KURU	KURU	KURU	KURU	0.022	0.164	KURU	0.012	KURU	KURU	KURU
23	KURU	KURU	KURU	KURU	KURU	0.022	0.213	KURU	0.012	KURU	KURU	KURU
24	KURU	KURU	KURU	KURU	KURU	0.022	0.213	0.012	0.012	KURU	KURU	KURU
25	KURU	KURU	KURU	KURU	KURU	0.022	0.263	KURU	0.012	KURU	KURU	KURU
26	KURU	KURU	KURU	KURU	KURU	0.022	0.213	KURU	0.012	KURU	KURU	KURU
27	KURU	KURU	KURU	KURU	KURU	0.022	0.213	KURU	0.012	KURU	KURU	KURU
28	KURU	KURU	KURU	KURU	KURU	0.022	0.213	KURU	0.012	KURU	KURU	KURU
29	KURU	KURU	KURU	KURU	-----	0.022	0.213	KURU	0.012	KURU	KURU	KURU
30	KURU	KURU	KURU	KURU	-----	0.022	0.213	KURU	0.012	KURU	KURU	KURU
31	KURU	-----	KURU	KURU	-----	0.022	-----	KURU	-----	KURU	KURU	-----
Maks.	KURU	KURU	KURU	KURU	KURU	0.022	0.263	0.361	0.012	KURU	KURU	KURU
Min.	KURU	KURU	KURU	KURU	KURU	KURU	0.022	KURU	KURU	KURU	KURU	KURU
Ortalama	KURU	KURU	KURU	KURU	KURU	0.011	0.125	0.075	0.007	KURU	KURU	KURU
LT/SN/Km2	0.000	0.000	0.000	0.000	0.000	0.428	4.72	2.84	0.257	0.000	0.000	0.000
AKIM mm.	0.000	0.000	0.000	0.000	0.000	1.15	12.2	7.61	0.665	0.000	0.000	0.000
MİL. M3	0.000	0.000	0.000	0.000	0.000	0.030	0.324	0.202	0.018	0.000	0.000	0.000

SU YILI (2006) YILLIK TOPLAM AKIM 0.57 MİLYON M3 22 MM. 0.7 LT/SN/Km2

18. Seyhan Havzasi

D18A051 EGNİ Ç. BÜYÜK SOFULU

YERİ : **ALADAĞ İLÇESİ BÜYÜKSOFULU-GERDİBİ KÖY YOLUNUN 4 KM SİNDEKİ EĞNİ SUYU KÖPRÜSÜNÜN 50 M MENBASINDADIR.**
35°9'15" Doğu - 37°33'8" Kuzey

YAĞIŞ ALANI : **114,80 km2** **YAKLAŞIK KOT : 916 m**

GÖZLEM SÜRESİ : **- 30.09.2006**

ORTALAMA AKIMLAR : **Gözlem süresinde 1.139 m3/sn. (2 Yıllık) 2006 Su yılında 1.373 m3/sn.**

ANLIK EN ÇOK VE EN AZ AKIMLAR:

2006 Su yılında anlık ençok akım	:	**9.96**	**m3/sn**	**02.04.2006**
2006 Su yılında anlık enaz akım	:	**0.079**	**m3/sn**	**01.10.2005**
Gözlem süresinde anlık ençok akım	:	**9.96**	**m3/sn**	**02.04.2006**
Gözlem süresinde anlık enaz akım	:	**0.058**	**m3/sn**	**01.10.2004**

Akımlar 01 Ekim 2005 'den 30 Eylül 2006' a kadar m3/sn olarak

Gün	Ekim	Kasım	Aralık	Ocak	Şubat	Mart	Nisan	Mayıs	Haziran	Temmuz	Ağustos	Eylül
01	0.100	0.369	1.56	0.854	0.771	2.17	4.97	1.56	0.937	0.610	0.270	0.191
02	0.100	0.270	1.56	0.854	0.771	2.17	7.50	1.68	1.12	0.610	0.270	0.191
03	0.100	0.270	1.56	0.854	0.771	2.33	6.08	1.93	1.04	0.610	0.317	0.191
04	0.100	1.56	1.45	0.771	0.771	2.48	5.19	1.93	1.04	0.547	0.317	0.191
05	0.100	1.34	1.45	0.771	0.771	2.64	4.57	1.80	1.04	0.854	0.369	0.191
06	0.100	1.23	1.23	0.771	0.771	2.64	4.21	1.80	1.04	0.691	0.317	0.191
07	0.100	1.23	1.12	0.771	1.12	2.79	4.39	1.68	1.56	0.691	0.317	0.191
08	0.100	1.34	1.04	0.771	1.80	2.95	4.75	1.56	4.39	0.691	0.317	0.191
09	0.100	1.45	0.937	0.771	1.93	2.95	5.19	1.56	4.39	0.691	0.317	0.158
10	0.124	1.45	0.854	0.771	1.68	2.48	6.52	1.68	4.03	0.691	0.270	0.191
11	0.124	1.45	0.937	0.771	1.80	2.33	6.08	1.68	1.68	0.691	0.270	0.191
12	0.124	1.45	0.937	0.691	1.93	2.17	5.19	1.80	0.854	0.854	0.317	0.158
13	0.124	1.34	0.854	0.691	1.80	2.33	5.19	1.93	0.854	0.771	0.317	0.191
14	0.158	1.23	0.854	0.691	1.68	2.95	5.19	1.80	0.854	0.771	0.317	0.231
15	0.158	1.23	0.854	0.691	1.56	3.31	4.75	1.80	0.691	0.771	0.270	0.231
16	0.191	1.23	0.854	0.691	1.34	3.13	4.57	1.80	0.691	0.771	0.270	0.231
17	0.270	1.12	0.854	0.691	1.23	3.13	4.57	1.68	0.691	0.484	0.270	0.191
18	0.270	1.12	1.34	0.691	1.12	3.13	4.03	1.56	0.610	0.369	0.231	0.231
19	0.317	1.12	3.31	0.691	1.12	3.31	3.67	1.56	0.610	0.317	0.231	0.231
20	0.317	1.68	2.48	0.771	1.23	3.13	3.85	1.56	0.610	0.317	0.231	0.231
21	0.317	3.31	2.05	0.691	1.34	2.95	3.67	1.68	0.547	0.317	0.270	0.231
22	0.317	2.64	1.68	0.691	1.45	3.13	3.13	1.80	0.547	0.270	0.270	0.231
23	0.317	2.17	1.45	0.691	1.80	4.21	3.13	1.80	0.547	0.369	0.270	0.231
24	0.270	1.80	1.34	0.691	2.05	5.41	2.95	1.68	0.547	0.369	0.231	0.231
25	0.270	1.56	1.12	0.854	2.05	6.52	2.48	1.45	0.547	0.427	0.231	0.270
26	0.270	1.56	1.04	0.937	2.33	5.63	2.05	1.34	0.547	0.369	0.270	0.270
27	0.270	1.56	1.04	0.937	2.33	4.97	1.80	1.34	0.547	0.369	0.231	0.270
28	0.270	1.56	0.937	0.937	2.17	4.75	1.80	1.12	0.547	0.317	0.191	0.317
29	0.270	1.56	0.854	0.937	-----	4.75	1.68	1.12	0.691	0.317	0.191	0.317
30	0.427	1.56	0.854	0.854	-----	4.97	1.56	1.04	0.610	0.317	0.191	0.369
31	0.369	-----	0.771	0.854	-----	4.97	-----	1.04	-----	0.317	0.191	-----
Maks.	0.547	3.85	5.19	1.04	2.64	8.30	9.96	1.93	6.30	0.854	0.427	0.427
Min.	0.079	0.270	0.771	0.691	0.691	2.05	1.56	1.04	0.547	0.231	0.158	0.158
Ortalama	0.208	1.43	1.26	0.778	1.48	3.44	4.16	1.61	1.15	0.534	0.269	0.224
LT/SN/Km2	1.81	12.4	11.0	6.77	12.9	30.0	36.2	14.0	9.99	4.65	2.34	1.95
AKIM mm.	4.85	32.2	29.5	18.1	31.2	80.4	93.9	37.5	25.9	12.5	6.28	5.07
MİL. M3	0.557	3.69	3.38	2.08	3.58	9.23	10.8	4.30	2.97	1.43	0.721	0.582

SU YILI (2006) YILLIK TOPLAM AKIM 43.32 MİLYON M3 377 MM. 12.0 LT/SN/Km2

19

ASİ HAVZASI

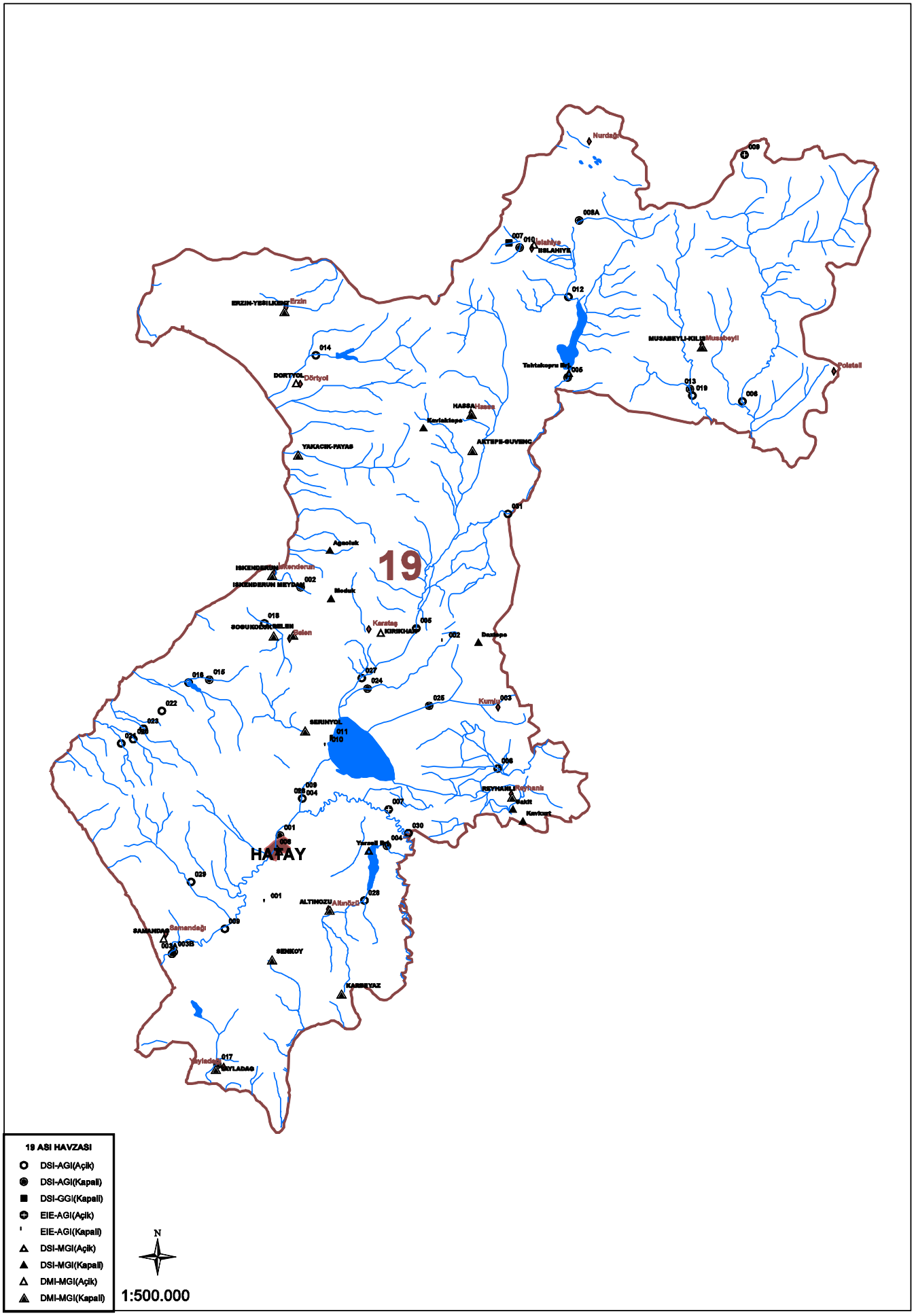
19
HATAY
Nurdağı
Erzin
Örtyol
Hassa
Musabeyli
Polatlı
Kırıkhan
Reyhanlı
Altınözü
Samandağı
19 ASI HAVZASI
DSI-AGI(Açik)
DSI-AGI(Kapali)
DSI-GGI(Kapali)
EIE-AGI(Açik)
EIE-AGI(Kapali)
DSI-MGI(Açik)
DSI-MGI(Kapali)
DMI-MGI(Açik)
DMI-MGI(Kapali)
N
1:500.000

19. Asi Havzasi

D19A008 EMEN ANA TAH. KAN. ÖRTÜLÜ

YERİ : **İslahiyeye 8 km mesafedeki örtülü köyündedir.**
36°42'53" Doğu - 37°3'32" Kuzey

YAĞIŞ ALANI : **0.00 km2** **YAKLAŞIK KOT : 464 m**

GÖZLEM SÜRESİ : **01.03.1980 - 30.09.2006**

ORTALAMA AKIMLAR : **Gözlem süresinde 1.080 m3/sn. (11 Yıllık) 2006 Su yılında 0.830 m3/sn.**

ANLIK EN ÇOK VE EN AZ AKIMLAR:

2006 Su yılında anlık ençok akım	:	**19.6**	**m3/sn**	**08.02.2006**
2006 Su yılında anlık enaz akım	:	**0.000**	**m3/sn**	**01.10.2005**
Gözlem süresinde anlık ençok akım	:	**22.8**	**m3/sn**	**26.03.2003**
Gözlem süresinde anlık enaz akım	:	**0.000**	**m3/sn**	**01.10.1982**

Akımlar 01 Ekim 2005 'den 30 Eylül 2006' a kadar m3/sn olarak

Gün	Ekim	Kasım	Aralık	Ocak	Şubat	Mart	Nisan	Mayıs	Haziran	Temmuz	Ağustos	Eylül
01	KURU	0.280	0.320	0.450	1.40	1.85	1.76	KURU	KURU	KURU	KURU	KURU
02	KURU	0.280	0.320	0.450	2.25	1.76	1.85	KURU	KURU	KURU	KURU	KURU
03	KURU	0.280	0.320	0.450	4.16	1.67	1.95	KURU	KURU	KURU	KURU	KURU
04	KURU	0.280	0.280	0.450	6.12	1.67	1.76	KURU	KURU	KURU	KURU	KURU
05	KURU	0.280	0.280	0.450	3.88	1.58	1.85	KURU	KURU	KURU	KURU	KURU
06	KURU	0.280	0.280	0.450	3.74	1.49	1.76	KURU	KURU	KURU	KURU	KURU
07	KURU	0.280	0.280	0.450	10.2	1.49	1.67	KURU	KURU	KURU	KURU	KURU
08	KURU	0.280	0.280	0.450	17.7	1.40	1.58	KURU	KURU	KURU	KURU	KURU
09	KURU	0.280	0.280	0.450	14.4	1.95	1.49	KURU	KURU	KURU	KURU	KURU
10	KURU	0.280	0.280	0.450	10.6	2.80	1.40	KURU	KURU	KURU	KURU	KURU
11	KURU	0.250	0.280	0.450	6.92	2.44	1.32	KURU	KURU	KURU	KURU	KURU
12	KURU	0.250	0.280	0.450	6.28	1.95	1.32	KURU	KURU	KURU	KURU	KURU
13	KURU	0.250	0.250	0.400	9.28	1.85	1.24	KURU	KURU	KURU	KURU	KURU
14	0.280	0.250	0.250	0.400	8.56	1.67	1.24	KURU	KURU	KURU	KURU	KURU
15	0.320	0.250	0.250	0.400	6.76	1.76	1.16	KURU	KURU	KURU	KURU	KURU
16	0.280	0.250	0.250	0.400	5.16	1.95	1.08	KURU	KURU	KURU	KURU	KURU
17	0.280	0.250	0.250	0.400	4.16	1.85	1.16	KURU	KURU	KURU	KURU	KURU
18	0.250	0.250	0.320	0.400	3.74	2.15	1.08	KURU	KURU	KURU	KURU	KURU
19	0.250	0.250	0.370	0.400	2.96	3.60	1.00	KURU	KURU	KURU	KURU	KURU
20	0.370	0.250	0.400	0.400	2.71	4.30	0.450	KURU	KURU	KURU	KURU	KURU
21	0.320	0.320	0.450	0.400	2.53	2.96	KURU	KURU	KURU	KURU	KURU	KURU
22	0.280	0.400	0.450	0.400	2.44	2.53	KURU	KURU	KURU	KURU	KURU	KURU
23	0.250	0.400	0.450	0.400	2.35	2.25	KURU	KURU	KURU	KURU	KURU	KURU
24	0.215	0.400	0.495	0.400	2.25	2.05	KURU	KURU	KURU	KURU	KURU	KURU
25	0.215	0.400	0.495	0.645	2.15	2.44	KURU	KURU	KURU	KURU	KURU	KURU
26	0.215	0.370	0.540	5.00	2.05	2.96	KURU	KURU	KURU	KURU	KURU	KURU
27	0.215	0.370	0.540	6.76	1.95	2.62	KURU	KURU	KURU	KURU	KURU	KURU
28	0.215	0.370	0.495	5.00	1.85	2.35	KURU	KURU	KURU	KURU	KURU	KURU
29	0.215	0.370	0.495	2.71	-----	2.35	KURU	KURU	KURU	KURU	KURU	KURU
30	0.250	0.320	0.450	1.85	-----	2.15	KURU	KURU	KURU	KURU	KURU	KURU
31	0.280	-----	0.450	1.49	-----	1.76	-----	KURU	-----	KURU	KURU	-----
Maks.	0.370	0.400	0.540	7.40	19.6	4.86	2.05	KURU	KURU	KURU	KURU	KURU
Min.	KURU	0.250	0.250	0.400	1.32	1.40	KURU	KURU	KURU	KURU	KURU	KURU
Ortalama	0.152	0.301	0.359	1.09	5.31	2.18	0.937	KURU	KURU	KURU	KURU	KURU
LT/SN/Km2	0.000	0.000	0.000	0.000	0.000	0.000	0.000	0.000	0.000	0.000	0.000	0.000
AKIM mm.	0.000	0.000	0.000	0.000	0.000	0.000	0.000	0.000	0.000	0.000	0.000	0.000
MİL. M3	0.406	0.779	0.962	2.91	12.8	5.84	2.43	0.000	0.000	0.000	0.000	0.000

SU YILI (2006) YILLIK TOPLAM AKIM 26.13 MİLYON M3 0 MM. 0.0 LT/SN/Km2

19. Asi Havzasi

D19A009 ASİ N. ÇÖĞÜRLÜ

YERİ : **ANTAKYA-SAMANDAĞI KARAYOLUNUN 22.KM.SİNDEN SAĞA AYRILAN SAMANDAĞI-YAYLADAĞI YOLUN ÜZERİNDEKİ ÇÖĞÜRLÜ KÖPRÜSÜNDEDİR.**
36°0'14" Doğu - 36°4'39" Kuzey

YAĞIŞ ALANI : **23205,00 km2** **YAKLAŞIK KOT : 11 m**

GÖZLEM SÜRESİ : **01.08.1968 - 30.09.2006**

ORTALAMA AKIMLAR : **Gözlem süresinde 68.394 m3/sn. (31 Yıllık) 2006 Su yılında 31.586 m3/sn.**

ANLIK EN ÇOK VE EN AZ AKIMLAR:

2006 Su yılında anlık ençok akım	**:**	**278.**	**m3/sn**	**13.02.2006**
2006 Su yılında anlık enaz akım	**:**	**0.000**	**m3/sn**	**16.06.2006**
Gözlem süresinde anlık ençok akım	**:**	**910.**	**m3/sn**	**21.05.1976**
Gözlem süresinde anlık enaz akım	**:**	**0.000**	**m3/sn**	**15.07.1999**

15. Anahtar Eğrisi (Seviyeler cm olarak)

Seviye	Akım	Seviye	Akım	Seviye	Akım	Seviye	Akım
1	0.230	30	30.2	180	348.	296	606.
4	1.9	60	74.6	213	425.	381	759.
7	4.2	90	132.	225	449.	406	804.
10	6.7	120	195.	230	464.	839	2070.
15	11.8	150	263.	243	491.		

Akımlar 01 Ekim 2005 'den 30 Eylül 2006' a kadar m3/sn olarak

Gün	Ekim	Kasım	Aralık	Ocak	Şubat	Mart	Nisan	Mayıs	Haziran	Temmuz	Ağustos	Eylül
01	16.0	29.0	21.4	29.0	86.4	54.3	55.4	19.4	1.60	KURU	KURU	KURU
02	18.1	29.0	21.4	27.5	78.3	46.7	63.4	19.4	1.60	KURU	KURU	KURU
03	20.1	28.2	20.7	26.7	74.8	49.9	63.4	20.1	2.91	KURU	KURU	KURU
04	20.1	34.5	20.7	26.0	68.0	48.8	70.2	20.1	2.20	KURU	KURU	KURU
05	20.7	29.8	20.1	25.2	64.5	46.7	79.4	19.4	1.32	KURU	KURU	KURU
06	20.1	32.0	20.1	25.2	62.3	47.8	87.6	18.8	1.32	KURU	KURU	KURU
07	19.4	32.0	20.1	24.6	68.0	45.6	87.6	18.1	1.15	KURU	KURU	KURU
08	19.4	32.0	20.1	25.2	134.	42.5	84.1	15.4	1.32	KURU	KURU	KURU
09	19.4	28.2	18.8	26.0	191.	40.5	77.1	13.2	1.32	KURU	KURU	KURU
10	28.2	26.0	16.0	25.2	164.	44.6	70.2	12.1	1.15	KURU	KURU	KURU
11	28.2	26.7	16.0	25.2	168.	47.8	65.7	11.0	1.15	KURU	KURU	KURU
12	28.2	26.0	16.7	28.2	175.	54.3	61.1	11.0	1.15	KURU	KURU	KURU
13	27.5	25.2	16.7	27.5	244.	62.3	55.4	10.4	1.15	KURU	KURU	KURU
14	19.4	24.6	17.4	28.2	218.	61.1	48.8	9.95	1.15	KURU	KURU	KURU
15	19.4	24.6	16.7	32.8	198.	62.3	41.4	9.49	2.20	KURU	KURU	KURU
16	20.7	25.2	20.1	38.8	177.	57.7	41.4	9.95	KURU	KURU	KURU	KURU
17	22.6	25.2	22.6	47.8	151.	55.4	45.6	9.49	KURU	KURU	KURU	KURU
18	20.1	22.6	29.0	57.7	141.	54.3	52.0	17.4	KURU	KURU	KURU	KURU
19	25.2	20.1	30.5	40.5	129.	119.	41.4	9.95	KURU	KURU	KURU	KURU
20	25.2	20.7	40.5	78.3	114.	95.8	36.2	4.21	KURU	KURU	KURU	16.7
21	26.0	32.8	35.4	66.8	95.8	84.1	27.5	3.20	KURU	KURU	KURU	9.04
22	25.2	24.6	32.8	70.2	87.6	78.3	27.5	2.91	KURU	KURU	KURU	11.5
23	24.6	25.2	32.8	92.3	81.8	72.5	27.5	2.91	KURU	KURU	KURU	13.2
24	24.6	25.2	36.2	97.0	77.1	65.7	23.3	2.55	KURU	KURU	KURU	14.3
25	25.2	23.9	41.4	107.	70.2	71.4	20.7	4.57	KURU	KURU	KURU	18.8
26	25.2	22.6	39.7	158.	66.8	179.	17.4	3.58	KURU	KURU	KURU	14.3
27	24.6	22.6	33.7	151.	63.4	97.0	16.0	7.25	KURU	KURU	KURU	17.4
28	25.2	22.0	33.7	134.	61.1	80.6	19.4	5.28	KURU	KURU	KURU	18.1
29	25.2	21.4	33.7	124.	-----	73.7	19.4	2.91	KURU	KURU	KURU	21.4
30	25.2	20.7	34.5	113.	-----	68.0	19.4	2.55	KURU	KURU	KURU	23.3
31	26.0	-----	32.0	98.2	-----	60.0	-----	2.20	-----	KURU	KURU	-----
Maks.	29.0	43.5	54.3	226.	278.	278.	88.8	20.7	2.91	KURU	KURU	25.2
Min.	14.3	19.4	16.0	24.6	60.0	38.8	15.4	2.20	KURU	KURU	KURU	KURU
Ortalama	23.1	26.1	26.2	60.6	118.	66.7	48.2	10.3	0.756	KURU	KURU	5.93
LT/SN/Km2	0.994	1.12	1.13	2.61	5.09	2.87	2.08	0.443	0.033	0.000	0.000	0.256
AKIM mm.	2.66	2.91	3.02	6.99	12.3	7.70	5.38	1.19	0.084	0.000	0.000	0.663
MİL. M3	61.8	67.6	70.1	162.	286.	179.	125.	27.5	1.96	0.000	0.000	15.4

SU YILI (2006) YILLIK TOPLAM AKIM 996.36 MİLYON M3 43 MM. 1.4 LT/SN/Km2

19. Asi Havzasi

D19A012 KARASU ÇOLAKLAR

YERİ : İSLAHİYE-HASSA KARAYOLUNUN 4.KM.SİNDEN SONRA SAĞA AYRILAN YOLUN 8.KM.SİNDE TAHTAKÖPRÜ MEVKİİNDEDİR.
36°41'20" Doğu - 36°57'32" Kuzey

YAĞIŞ ALANI : 478,00 km2 **YAKLAŞIK KOT** : 455 m

GÖZLEM SÜRESİ : 01.12.1973 - 30.09.2006

ORTALAMA AKIMLAR : Gözlem süresinde 3.679 m3/sn. (27 Yıllık) 2006 Su yılında 3.240 m3/sn.

ANLIK EN ÇOK VE EN AZ AKIMLAR:

2006 Su yılında anlık ençok akım	:	73.6	m3/sn	08.02.2006
2006 Su yılında anlık enaz akım	:	0.030	m3/sn	08.07.2006
Gözlem süresinde anlık ençok akım	:	105.	m3/sn	28.03.1980
Gözlem süresinde anlık enaz akım	:	0.000	m3/sn	19.08.1982

4. Anahtar Eğrisi (Seviyeler cm olarak)

Seviye	Akım	Seviye	Akım	Seviye	Akım	Seviye	Akım
1	0.000	39	0.030	80	1.8	151	12.0
7	0.000	52	0.230	86	2.2	211	32.0
13	0.000	62	0.660	92	2.8	271	68.0
19	0.000	68	1.0	98	3.2	331	130.
25	0.000	74	1.4	116	5.4	391	220.

Akımlar 01 Ekim 2005 'den 30 Eylül 2006' a kadar m3/sn olarak

Gün	Ekim	Kasım	Aralık	Ocak	Şubat	Mart	Nisan	Mayıs	Haziran	Temmuz	Ağustos	Eylül
01	0.660	0.910	1.00	1.70	3.20	5.40	6.20	1.10	1.40	0.230	0.053	0.045
02	0.720	0.910	1.00	1.60	9.00	5.56	7.20	0.720	1.50	0.200	0.053	0.045
03	0.770	1.00	1.50	1.50	10.6	5.72	7.68	0.720	1.35	0.200	0.045	0.060
04	0.770	1.00	1.10	1.50	8.80	6.80	6.80	0.660	1.40	0.180	0.045	0.060
05	0.600	1.10	1.50	1.50	8.40	7.00	8.00	0.500	1.35	0.200	0.045	0.080
06	0.600	1.05	1.65	1.50	13.8	6.04	7.36	0.450	1.30	0.160	0.045	0.070
07	0.660	1.05	1.65	1.50	45.6	5.56	6.40	0.770	1.25	0.135	0.045	0.180
08	0.660	1.05	1.65	1.50	66.4	5.72	5.88	1.15	1.10	0.053	0.045	0.400
09	0.660	1.05	1.65	1.40	49.8	10.0	5.56	0.910	1.10	0.038	0.045	0.200
10	0.660	1.00	1.60	1.40	35.5	11.4	5.16	0.720	1.00	0.060	0.045	0.250
11	0.720	1.00	1.20	1.40	22.7	8.40	4.80	0.400	0.400	0.045	0.053	0.160
12	0.660	1.00	1.15	1.40	18.2	7.20	4.44	0.550	0.450	0.053	0.060	0.180
13	0.660	1.00	1.20	1.40	33.5	6.20	4.20	0.720	0.450	0.053	0.053	0.160
14	0.720	1.05	1.20	1.40	33.5	5.72	4.08	1.15	0.350	0.030	0.060	0.200
15	0.720	1.00	1.20	1.35	24.6	6.60	3.84	1.00	0.280	0.053	0.053	0.200
16	0.910	1.05	1.30	1.05	17.6	9.20	3.72	1.00	0.300	0.053	0.053	0.200
17	1.05	1.05	5.72	1.25	12.6	8.40	4.44	0.820	0.280	0.030	0.053	0.230
18	1.20	1.05	6.04	1.30	10.6	7.52	3.72	0.910	0.230	0.030	0.053	0.250
19	1.30	1.05	4.80	1.30	9.00	19.1	3.20	1.05	0.230	0.053	0.070	0.300
20	1.15	1.05	3.00	2.10	7.84	17.9	3.20	0.910	0.200	0.080	0.045	0.350
21	1.10	1.70	2.60	2.60	7.20	13.4	2.10	0.770	0.095	0.070	0.060	0.450
22	0.910	1.35	2.60	1.90	6.60	10.8	2.10	0.820	0.080	0.080	0.070	0.450
23	0.600	1.25	2.60	1.90	6.20	9.00	2.00	1.05	0.080	0.070	0.060	0.500
24	0.770	1.20	3.10	2.40	6.20	8.00	1.70	0.910	0.135	0.095	0.070	0.450
25	0.820	1.20	3.96	4.68	6.04	7.84	1.65	1.00	0.110	0.095	0.053	0.550
26	0.820	1.20	3.20	18.2	5.88	13.0	1.65	1.00	0.180	0.095	0.053	0.600
27	0.820	1.15	3.20	22.4	5.72	11.8	1.60	1.05	0.110	0.070	0.053	0.600
28	0.910	1.15	3.20	10.8	5.40	9.80	1.60	1.00	0.110	0.060	0.053	0.720
29	1.00	1.05	2.40	6.04	-----	8.80	1.50	1.05	0.180	0.045	0.053	0.720
30	0.910	1.05	2.70	4.20	-----	7.52	1.50	1.10	0.200	0.045	0.045	0.720
31	0.910	-----	1.90	3.30	-----	7.00	-----	1.35	-----	0.045	0.045	-----
Maks.	2.50	3.30	7.00	31.5	73.6	26.2	8.60	2.10	1.60	0.280	0.110	1.25
Min.	0.160	0.910	0.820	0.450	3.10	5.40	1.35	0.400	0.070	0.030	0.045	0.045
Ortalama	0.820	1.09	2.34	3.47	17.5	8.79	4.11	0.881	0.573	0.087	0.053	0.313
LT/SN/Km2	1.72	2.28	4.90	7.25	36.6	18.4	8.60	1.84	1.20	0.183	0.110	0.654
AKIM mm.	4.59	5.91	13.1	19.4	88.7	49.2	22.3	4.94	3.11	0.489	0.295	1.70
MİL. M3	2.20	2.83	6.27	9.29	42.4	23.5	10.7	2.36	1.49	0.234	0.141	0.810

SU YILI (2006) YILLIK TOPLAM AKIM 102.22 MİLYON M3 214 MM. 6.8 LT/SN/Km2

19. Asi Havzasi

D19A014 DELİÇAY MUTLU ÇUKUR

YERİ : **ERZİN DÖRTYOL KARAYOLU ÜZERİNDEKİ KUZUÇULAR BELDESİDENİN 1 KM. KUZEYİNDEN SAĞA AYRILAN HAM YOLUN 4.KM SİNDEKİ MUTLUÇUKUR MEVKİİNDEDİR. (O36-B1)**
36°15'4" Doğu - 36°53'17" Kuzey

YAĞIŞ ALANI : **161,50 km2** **YAKLAŞIK KOT : 200 m**

GÖZLEM SÜRESİ : **01.11.1976 - 30.09.2006**

ORTALAMA AKIMLAR : **Gözlem süresinde 3.913 m3/sn. (26 Yıllık) 2006 Su yılında 3.121 m3/sn.**

ANLIK EN ÇOK VE EN AZ AKIMLAR:

2006 Su yılında anlık ençok akım	:	**14.8**	**m3/sn**	**19.03.2006**
2006 Su yılında anlık enaz akım	:	**0.280**	**m3/sn**	**13.07.2006**
Gözlem süresinde anlık ençok akım	:	**92.0**	**m3/sn**	**08.01.1982**
Gözlem süresinde anlık enaz akım	:	**0.280**	**m3/sn**	**13.07.2006**

13. Anahtar Eğrisi (Seviyeler cm olarak)

Seviye	Akım	Seviye	Akım	Seviye	Akım	Seviye	Akım
72	0.185	140	16.8	210	48.5	260	77.0
76	0.495	160	24.7	220	54.0	270	82.0
80	1.1	180	33.7	230	60.0	280	88.0
100	5.0	190	38.4	240	66.0	290	94.0
120	10.5	200	43.3	250	72.0	300	98.0

Akımlar 01 Ekim 2005 'den 30 Eylül 2006' a kadar m3/sn olarak

Gün	Ekim	Kasım	Aralık	Ocak	Şubat	Mart	Nisan	Mayıs	Haziran	Temmuz	Ağustos	Eylül
01	1.13	1.20	1.27	1.67	2.78	6.03	7.39	4.95	2.23	1.85	1.30	1.85
02	1.13	1.20	1.27	1.67	2.97	6.58	9.08	4.55	2.23	2.23	1.30	1.85
03	1.13	1.20	1.27	1.48	2.97	6.31	8.23	5.49	2.04	2.04	1.30	1.85
04	1.13	1.20	1.27	1.48	2.78	7.66	6.31	5.76	2.04	2.23	1.30	1.85
05	1.05	1.20	1.27	1.48	2.78	5.76	7.12	5.76	2.04	2.60	1.30	1.85
06	1.05	1.20	1.27	1.30	3.17	5.22	8.23	5.49	2.04	2.41	1.30	1.67
07	1.05	1.20	1.27	1.30	4.95	5.49	9.08	4.95	2.04	2.41	1.30	1.67
08	1.05	1.20	1.27	1.30	6.85	6.58	9.08	4.75	2.04	2.23	1.30	1.48
09	1.05	1.20	1.05	1.30	6.03	7.66	9.36	4.75	2.04	2.23	1.30	1.48
10	0.970	1.13	0.970	1.11	6.31	7.12	9.65	4.36	2.04	2.23	1.30	1.30
11	0.970	1.20	0.868	1.11	6.31	6.31	9.36	3.96	1.85	2.23	1.30	1.11
12	0.970	1.20	0.868	1.11	6.31	6.85	9.08	3.96	1.85	2.23	1.30	1.11
13	0.970	1.20	0.970	1.11	7.39	6.85	9.36	3.96	1.85	1.85	1.30	1.11
14	0.970	1.20	0.970	1.11	8.23	6.58	9.36	3.76	1.85	1.85	1.30	1.11
15	0.970	1.20	0.970	1.11	7.94	7.66	9.36	3.56	1.85	1.85	1.30	1.11
16	1.05	1.20	0.970	0.960	6.58	8.51	9.65	3.56	1.67	1.85	1.30	1.11
17	1.49	1.20	5.85	0.960	5.22	7.94	11.1	4.16	1.67	1.67	1.30	1.11
18	1.27	1.20	6.49	0.960	4.16	7.66	10.2	3.76	1.67	1.67	1.30	1.11
19	3.21	1.20	5.01	0.960	4.36	10.8	9.36	3.37	1.67	1.67	1.30	1.11
20	1.82	1.20	4.36	3.17	4.36	8.80	8.80	3.37	1.67	1.67	1.30	1.11
21	1.20	1.49	4.16	2.97	4.55	6.85	8.23	3.17	1.48	1.67	1.11	1.11
22	1.20	2.16	3.17	2.60	5.22	5.49	7.66	3.17	1.48	1.67	1.11	1.30
23	1.20	1.49	2.97	2.97	5.76	5.49	8.23	3.56	2.04	1.67	1.30	1.30
24	1.20	1.27	2.78	2.60	5.49	6.03	8.80	3.17	2.04	1.67	1.67	1.30
25	1.20	1.27	2.60	2.97	6.31	6.58	7.39	2.97	2.04	1.30	1.85	1.11
26	1.20	1.27	2.41	4.36	6.03	9.93	7.12	2.97	1.85	1.30	1.48	1.11
27	1.20	1.27	2.41	4.55	6.03	8.80	6.31	2.78	1.85	1.30	1.30	1.11
28	1.20	1.27	2.41	3.96	5.76	7.94	5.76	2.78	1.85	1.30	1.30	0.960
29	1.20	1.27	2.04	3.37	-----	7.39	5.22	2.60	1.67	1.30	1.30	0.960
30	1.20	1.27	1.85	3.17	-----	7.12	5.22	2.60	2.04	1.30	1.48	0.960
31	1.20	-----	1.85	2.97	-----	6.85	-----	2.41	-----	1.30	1.85	-----
Maks.	3.61	2.70	8.49	6.85	8.80	14.8	14.1	6.58	2.41	3.37	2.23	2.04
Min.	0.688	1.05	0.868	0.960	2.78	4.95	4.95	2.23	1.48	0.280	0.280	0.653
Ortalama	1.21	1.27	2.20	2.04	5.27	7.12	8.30	3.88	1.89	1.83	1.35	1.31
LT/SN/Km2	7.52	7.83	13.6	12.6	32.6	44.1	51.4	24.1	11.7	11.3	8.34	8.08
AKIM mm.	20.1	20.3	36.5	33.8	79.0	118.	133.	64.4	30.3	30.4	22.3	21.0
MİL. M3	3.25	3.28	5.89	5.46	12.8	19.1	21.5	10.4	4.90	4.91	3.61	3.38

SU YILI (2006) YILLIK TOPLAM AKIM 98.48 MİLYON M3 610 MM. 19.3 LT/SN/Km2

19. Asi Havzasi

D19A016 GÖNEN Ç. ADA MAHALLESİ

YERİ : İSKENDERUN ARSUZ YOLUNUN 25.KM SİNDEN SOLA AYRILAN MADENLİ KÖYÜNÜN 4.KM DOĞUSUNDAKİ ADA MAHALLESİNDEDİR. (P36 - A1)
36°1'8" Doğu - 36°26'16" Kuzey

YAĞIŞ ALANI : 94,00 km2 **YAKLAŞIK KOT** : 240 m

GÖZLEM SÜRESİ : 06.10.1977 - 30.09.2006

ORTALAMA AKIMLAR : Gözlem süresinde 1.426 m3/sn. (24 Yıllık) 2006 Su yılında 0.973 m3/sn.

ANLIK EN ÇOK VE EN AZ AKIMLAR:

2006 Su yılında anlık ençok akım	:	31.5	m3/sn	08.02.2006
2006 Su yılında anlık enaz akım	:	0.066	m3/sn	02.08.2006
Gözlem süresinde anlık ençok akım	:	78.4	m3/sn	17.12.2003
Gözlem süresinde anlık enaz akım	:	0.010	m3/sn	10.07.1991

15. Anahtar Eğrisi (Seviyeler cm olarak)

Seviye	Akım	Seviye	Akım	Seviye	Akım	Seviye	Akım
1	0.000	33	3.3	65	19.0	121	56.0
5	0.049	37	4.8	73	24.0	131	64.0
9	0.134	41	6.2	81	29.0	141	68.0
14	0.291	49	10.0	89	36.0		
27	1.9	57	14.5	97	40.0		

Akımlar 01 Ekim 2005 'den 30 Eylül 2006' a kadar m3/sn olarak

Gün	Ekim	Kasım	Aralık	Ocak	Şubat	Mart	Nisan	Mayıs	Haziran	Temmuz	Ağustos	Eylül
01	0.117	0.199	0.356	0.586	1.17	1.73	2.06	0.828	0.266	0.199	0.139	0.066
02	0.117	0.266	0.356	0.586	1.17	1.89	3.00	0.667	0.230	0.199	0.066	0.066
03	0.117	0.667	0.356	0.523	1.17	1.89	3.30	0.667	0.230	0.199	0.066	0.066
04	0.117	1.17	0.356	0.523	1.30	1.89	2.70	0.667	0.230	0.199	0.066	0.066
05	0.117	0.667	0.302	0.523	1.42	1.73	2.70	0.586	0.302	0.199	0.066	0.066
06	0.117	1.17	0.302	0.523	1.58	1.58	2.70	0.586	0.266	0.266	0.066	0.066
07	0.117	1.05	0.302	0.523	3.70	1.58	2.40	0.586	0.266	0.266	0.066	0.066
08	0.117	0.748	0.302	0.523	22.5	1.58	2.23	0.586	0.266	0.266	0.066	0.066
09	0.117	0.586	0.398	0.523	11.0	2.40	1.89	0.523	0.266	0.266	0.066	0.066
10	0.117	0.460	0.398	0.523	4.40	2.23	1.89	0.523	0.398	0.169	0.066	0.066
11	0.117	0.356	0.398	0.523	3.30	2.06	1.73	0.460	0.302	0.117	0.066	0.066
12	0.117	0.302	0.460	0.828	5.80	1.89	1.73	0.460	0.266	0.117	0.066	0.066
13	0.117	0.266	0.356	1.17	15.3	1.73	1.42	0.523	0.266	0.139	0.066	0.066
14	0.117	0.266	0.266	1.30	7.50	1.73	1.42	0.586	0.266	0.139	0.066	0.066
15	0.117	0.398	0.199	0.908	5.40	1.89	1.30	0.586	0.266	0.139	0.066	0.066
16	0.117	0.356	0.199	0.828	4.80	1.73	1.30	0.586	0.266	0.139	0.066	0.066
17	0.117	0.302	0.199	0.748	4.00	1.73	1.30	0.586	0.266	0.139	0.066	0.066
18	0.117	0.302	0.230	0.748	3.00	1.73	1.30	0.748	0.266	0.139	0.066	0.066
19	0.266	0.302	0.586	0.667	2.70	3.70	1.17	0.667	0.266	0.139	0.066	0.066
20	0.139	0.908	1.58	5.00	2.40	4.80	1.17	0.586	0.199	0.139	0.066	0.066
21	0.091	0.828	1.05	4.80	2.23	3.70	1.05	0.586	0.199	0.139	0.066	0.066
22	0.139	0.667	0.908	1.89	2.06	3.00	1.05	0.586	0.199	0.139	0.066	0.066
23	0.117	0.586	1.05	1.42	1.89	2.40	1.05	0.523	0.199	0.139	0.066	0.091
24	0.117	0.523	1.42	1.17	1.89	2.40	0.908	0.523	0.199	0.139	0.066	0.199
25	0.117	0.523	1.58	1.89	1.73	2.40	0.908	0.302	0.199	0.139	0.066	0.139
26	0.117	0.460	1.17	4.00	1.73	4.00	0.908	0.266	0.199	0.139	0.066	0.091
27	0.117	0.460	0.908	3.70	1.73	4.00	0.908	0.266	0.199	0.139	0.066	0.091
28	0.117	0.460	0.828	2.23	1.58	3.00	0.828	0.230	0.199	0.139	0.066	0.091
29	0.117	0.398	0.748	1.73	-----	2.40	0.828	0.302	0.199	0.139	0.066	0.091
30	0.117	0.398	0.748	1.58	-----	2.23	0.828	0.266	0.199	0.139	0.066	0.066
31	0.117	-----	0.667	1.30	-----	2.23	-----	0.266	-----	0.139	0.066	-----
Maks.	0.748	1.89	3.00	30.0	31.5	10.5	4.80	0.828	0.460	0.266	0.139	0.586
Min.	0.091	0.117	0.199	0.523	1.17	1.58	0.828	0.230	0.199	0.117	0.066	0.066
Ortalama	0.122	0.535	0.612	1.41	4.23	2.36	1.60	0.520	0.245	0.165	0.068	0.077
LT/SN/Km2	1.30	5.69	6.51	15.0	45.0	25.1	17.0	5.53	2.60	1.75	0.727	0.820
AKIM mm.	3.49	14.7	17.4	40.2	109.	67.3	44.1	14.8	6.75	4.69	1.95	2.12
MİL. M3	0.328	1.39	1.64	3.78	10.2	6.33	4.15	1.39	0.634	0.441	0.183	0.200

SU YILI (2006) YILLIK TOPLAM AKIM 30.67 MİLYON M3 326 MM. 10.4 LT/SN/Km2

19. Asi Havzasi

D19A018 Derebahçe D. Müftü Köp.

YERİ : **İSKENDERUN-ANTAKYA YOLUNUN 10.KM.SİNDEN SAĞA AYRILAN HAMYOLUN 1.5 KM.SİNDEKİ MÜFTÜLER KÖPRÜSÜNDEDİR.**
36°9'3" Doğu - 36°31'3" Kuzey

YAĞIŞ ALANI : **61,00 km2** **YAKLAŞIK KOT : 165 m**

GÖZLEM SÜRESİ : **13.03.1979 - 30.09.2006**

ORTALAMA AKIMLAR : **Gözlem süresinde 0.502 m3/sn. (18 Yıllık) 2006 Su yılında 0.188 m3/sn.**

ANLIK EN ÇOK VE EN AZ AKIMLAR:

2006 Su yılında anlık ençok akım	:	**3.68**	**m3/sn**	**13.02.2006**
2006 Su yılında anlık enaz akım	:	**0.004**	**m3/sn**	**11.09.2006**
Gözlem süresinde anlık ençok akım	:	**38.8**	**m3/sn**	**26.03.2003**
Gözlem süresinde anlık enaz akım	:	**0.000**	**m3/sn**	**01.08.1979**

15. Anahtar Eğrisi (Seviyeler cm olarak)

Seviye	Akım	Seviye	Akım	Seviye	Akım	Seviye	Akım
10	0.001	31	0.117	59	1.7	110	18.6
15	0.006	35	0.189	63	2.3	120	23.4
18	0.013	42	0.432	72	3.9	130	28.4
21	0.024	46	0.596	82	6.4	140	33.7
26	0.058	53	1.1	100	14.2	150	39.4

Akımlar 01 Ekim 2005 'den 30 Eylül 2006' a kadar m3/sn olarak

Gün	Ekim	Kasım	Aralık	Ocak	Şubat	Mart	Nisan	Mayıs	Haziran	Temmuz	Ağustos	Eylül
01	0.117	0.036	0.058	0.106	0.339	0.596	0.432	0.241	0.058	0.058	0.030	0.009
02	0.117	0.051	0.058	0.084	0.339	0.596	0.432	0.241	0.071	0.058	0.030	0.009
03	0.084	0.043	0.071	0.084	0.339	0.596	0.432	0.215	0.051	0.058	0.024	0.009
04	0.084	0.084	0.071	0.084	0.339	0.596	0.432	0.215	0.051	0.058	0.024	0.009
05	0.071	0.058	0.071	0.084	0.339	0.596	0.432	0.189	0.051	0.051	0.024	0.008
06	0.071	0.058	0.071	0.071	0.339	0.596	0.432	0.215	0.058	0.051	0.024	0.009
07	0.058	0.058	0.071	0.071	0.432	0.596	0.432	0.189	0.051	0.051	0.020	0.009
08	0.058	0.058	0.071	0.071	1.70	0.596	0.432	0.215	0.051	0.043	0.020	0.009
09	0.051	0.058	0.071	0.058	1.38	0.556	0.432	0.215	0.051	0.043	0.020	0.009
10	0.051	0.058	0.106	0.058	1.00	0.516	0.432	0.189	0.058	0.036	0.016	0.009
11	0.043	0.058	0.215	0.058	0.713	0.516	0.432	0.173	0.058	0.036	0.016	0.008
12	0.036	0.058	0.137	0.058	0.713	0.516	0.432	0.173	0.058	0.030	0.013	0.009
13	0.030	0.058	0.117	0.058	1.59	0.516	0.432	0.173	0.058	0.024	0.013	0.009
14	0.030	0.058	0.106	0.071	1.08	0.432	0.432	0.173	0.058	0.020	0.013	0.009
15	0.030	0.058	0.095	0.071	1.00	0.432	0.432	0.106	0.058	0.020	0.013	0.013
16	0.043	0.058	0.095	0.071	0.849	0.432	0.432	0.095	0.051	0.016	0.013	0.013
17	0.051	0.058	0.095	0.071	0.713	0.556	0.556	0.095	0.043	0.016	0.013	0.016
18	0.043	0.058	0.106	0.071	0.713	0.556	0.556	0.106	0.043	0.016	0.013	0.016
19	0.084	0.058	0.106	0.084	0.713	0.516	0.474	0.137	0.051	0.013	0.013	0.020
20	0.051	0.058	0.106	0.556	0.713	0.516	0.432	0.117	0.051	0.020	0.013	0.020
21	0.051	0.095	0.095	0.386	0.655	0.432	0.339	0.106	0.051	0.020	0.016	0.024
22	0.051	0.071	0.095	0.215	0.596	0.432	0.339	0.095	0.051	0.016	0.013	0.024
23	0.051	0.071	0.095	0.215	0.596	0.386	0.293	0.095	0.051	0.013	0.013	0.024
24	0.051	0.071	0.095	0.215	0.596	0.386	0.293	0.095	0.043	0.013	0.013	0.051
25	0.043	0.071	0.095	0.432	0.596	0.386	0.293	0.084	0.043	0.013	0.009	0.058
26	0.036	0.058	0.095	0.849	0.596	0.386	0.293	0.084	0.043	0.013	0.009	0.058
27	0.036	0.058	0.095	1.08	0.596	0.339	0.267	0.071	0.071	0.013	0.009	0.084
28	0.036	0.058	0.095	0.474	0.596	0.339	0.267	0.084	0.051	0.013	0.009	0.084
29	0.036	0.058	0.095	0.386	-----	0.339	0.267	0.095	0.051	0.013	0.009	0.095
30	0.036	0.058	0.084	0.339	-----	0.339	0.241	0.071	0.071	0.013	0.009	0.084
31	0.036	-----	0.106	0.339	-----	0.386	-----	0.071	-----	0.013	0.009	-----
Maks.	0.772	0.849	0.432	1.97	3.68	0.849	0.849	0.267	0.137	0.071	0.036	0.117
Min.	0.030	0.036	0.030	0.051	0.339	0.293	0.241	0.071	0.043	0.008	0.008	0.004
Ortalama	0.054	0.060	0.095	0.222	0.720	0.483	0.394	0.143	0.054	0.028	0.016	0.027
LT/SN/Km2	0.881	0.990	1.56	3.63	11.8	7.92	6.46	2.34	0.878	0.461	0.255	0.442
AKIM mm.	2.36	2.57	4.17	9.73	28.6	21.2	16.7	6.26	2.27	1.23	0.684	1.14
MİL. M3	0.144	0.156	0.254	0.594	1.74	1.29	1.02	0.382	0.139	0.075	0.042	0.070

SU YILI (2006) YILLIK TOPLAM AKIM 5.91 MİLYON M3 97 MM. 3.1 LT/SN/Km2

19. Asi Havzasi

D19A019 Sabun S. Günesli

YERİ : **KİLİS HASSA YOLUNUN 75.KM SINDEN GÜNESLI KÖYÜNE AYRILAN YOL UZERINDEKI SABUN SUYU KÖPRÜSÜNÜN YAKLAŞIK 250 M MEMBASINDADIR.**
36°53'47" Doğu - 36°48'48" Kuzey

YAĞIŞ ALANI : **276.00 km2** **YAKLAŞIK KOT : 446 m**

GÖZLEM SÜRESİ : **01.02.1984 - 30.09.2006**

ORTALAMA AKIMLAR : **Gözlem süresinde 1.420 m3/sn. (15 Yıllık) 2006 Su yılında 0.953 m3/sn.**

ANLIK EN ÇOK VE EN AZ AKIMLAR:

2006 Su yılında anlık ençok akım	:	**27.6**	**m3/sn**	**08.02.2006**
2006 Su yılında anlık enaz akım	:	**0.000**	**m3/sn**	**24.06.2006**
Gözlem süresinde anlık ençok akım	:	**94.5**	**m3/sn**	**18.02.1990**
Gözlem süresinde anlık enaz akım	:	**0.000**	**m3/sn**	**01.10.1986**

Akımlar 01 Ekim 2005 'den 30 Eylül 2006' a kadar m3/sn olarak

Gün	Ekim	Kasım	Aralık	Ocak	Şubat	Mart	Nisan	Mayıs	Haziran	Temmuz	Ağustos	Eylül
01	KURU	0.021	0.127	0.338	0.892	1.80	2.43	0.807	0.179	KURU	KURU	KURU
02	KURU	0.021	0.100	0.284	2.62	1.65	3.21	0.723	0.153	KURU	KURU	KURU
03	KURU	0.021	0.100	0.284	3.95	1.65	3.46	0.638	0.153	KURU	KURU	KURU
04	KURU	0.100	0.100	0.284	2.43	1.51	3.01	0.638	0.153	KURU	KURU	KURU
05	KURU	0.100	0.100	0.258	2.09	1.51	3.95	0.554	0.153	KURU	KURU	KURU
06	KURU	0.127	0.100	0.258	5.41	1.51	3.21	0.554	0.153	KURU	KURU	KURU
07	KURU	0.127	0.100	0.258	5.09	1.51	2.82	0.500	0.127	KURU	KURU	KURU
08	KURU	0.127	0.100	0.232	25.2	1.40	2.43	0.500	0.127	KURU	KURU	KURU
09	KURU	0.100	0.100	0.232	16.2	2.23	2.23	0.446	0.127	KURU	KURU	KURU
10	KURU	0.100	0.100	0.232	8.30	2.62	2.09	0.446	0.127	KURU	KURU	KURU
11	KURU	0.074	0.100	0.258	6.38	2.23	1.94	0.446	0.100	KURU	KURU	KURU
12	KURU	0.074	0.100	0.258	5.74	1.94	1.94	0.392	0.074	KURU	KURU	KURU
13	KURU	0.074	0.100	0.500	16.6	1.80	1.80	0.392	0.074	KURU	KURU	KURU
14	KURU	0.047	0.100	0.284	11.9	1.65	1.65	0.392	0.047	KURU	KURU	KURU
15	KURU	0.047	0.100	0.258	7.65	2.09	1.65	0.338	0.021	KURU	KURU	KURU
16	KURU	0.047	0.127	0.258	6.06	1.94	1.51	0.338	0.013	KURU	KURU	KURU
17	KURU	0.017	0.205	0.258	5.09	1.80	1.65	0.338	0.013	KURU	KURU	KURU
18	KURU	0.009	0.284	0.258	4.44	1.80	1.51	0.338	0.013	KURU	KURU	KURU
19	0.005	0.017	0.338	0.284	3.95	3.21	1.40	0.284	0.009	KURU	KURU	KURU
20	0.100	0.179	0.284	1.94	3.46	4.44	1.30	0.284	0.009	KURU	KURU	KURU
21	0.074	0.258	0.284	2.43	3.21	2.43	1.19	0.284	0.001	KURU	KURU	KURU
22	0.021	0.232	0.258	1.08	3.01	1.94	1.08	0.284	0.001	KURU	KURU	KURU
23	0.017	0.205	0.500	0.892	2.62	1.80	1.08	0.284	KURU	KURU	KURU	KURU
24	0.013	0.205	0.723	0.892	2.43	1.80	1.08	0.258	KURU	KURU	KURU	KURU
25	0.013	0.179	1.51	1.80	2.23	2.23	1.08	0.258	KURU	KURU	KURU	KURU
26	0.005	0.153	1.08	5.41	2.23	5.09	1.08	0.232	KURU	KURU	KURU	KURU
27	0.001	0.153	0.807	5.09	2.09	3.95	0.976	0.179	KURU	KURU	KURU	KURU
28	0.001	0.127	0.638	2.09	1.94	3.21	0.892	0.179	KURU	KURU	KURU	KURU
29	0.001	0.127	0.500	1.65	-----	3.01	0.892	0.153	KURU	KURU	KURU	KURU
30	0.021	0.127	0.446	1.30	-----	2.82	0.807	0.153	KURU	KURU	KURU	KURU
31	0.021	-----	0.392	1.08	-----	2.62	-----	0.179	-----	KURU	KURU	-----
Maks.	0.127	0.392	1.80	6.70	27.6	6.06	4.44	0.807	0.179	KURU	KURU	KURU
Min.	0.001	0.005	0.100	0.232	0.892	1.40	0.807	0.153	KURU	KURU	KURU	KURU
Ortalama	0.009	0.106	0.319	0.998	5.83	2.30	1.84	0.380	0.061	KURU	KURU	KURU
LT/SN/Km2	0.034	0.386	1.16	3.62	21.1	8.32	6.68	1.38	0.221	0.000	0.000	0.000
AKIM mm.	0.092	1.00	3.10	9.68	51.1	22.3	17.3	3.69	0.572	0.000	0.000	0.000
MİL. M3	0.025	0.276	0.856	2.67	14.1	6.15	4.78	1.02	0.158	0.000	0.000	0.000

SU YILI (2006) YILLIK TOPLAM AKIM 30.04 MİLYON M3 109 MM. 3.5 LT/SN/Km2

19. Asi Havzasi

D19A020 HÜYÜK D. HÜYÜK

YERİ : İSKENDERUN-ARSUZ BELDESİNİN 10.KM.GÜNEYDOĞUSUNDAKİ HÖYÜK KÖYÜNDEDİR.
35°55'20" Doğu - 36°21'40" Kuzey

YAĞIŞ ALANI : 35,00 km2 **YAKLAŞIK KOT** : 80 m

GÖZLEM SÜRESİ : 01.08.1985 - 30.09.2006

ORTALAMA AKIMLAR : Gözlem süresinde 1.352 m3/sn. (20 Yıllık) 2006 Su yılında 0.752 m3/sn.

ANLIK EN ÇOK VE EN AZ AKIMLAR:

2006 Su yılında anlık ençok akım	:	28.8	m3/sn	27.03.2006
2006 Su yılında anlık enaz akım	:	0.029	m3/sn	18.12.2005
Gözlem süresinde anlık ençok akım	:	160.	m3/sn	07.05.2001
Gözlem süresinde anlık enaz akım	:	0.010	m3/sn	31.05.1999

1. Anahtar Eğrisi (Seviyeler cm olarak)

Seviye	Akım	Seviye	Akım	Seviye	Akım	Seviye	Akım
18	0.013	65	15.5	115	46.0	165	88.0
25	0.280	75	21.0	125	55.0	175	96.0
35	2.1	85	28.0	135	63.0	180	100.
45	5.6	95	35.0	145	72.0	190	110.
55	10.0	105	40.0	155	80.0	200	120.

Akımlar 01 Ekim 2005 'den 30 Eylül 2006' a kadar m3/sn olarak

Gün	Ekim	Kasım	Aralık	Ocak	Şubat	Mart	Nisan	Mayıs	Haziran	Temmuz	Ağustos	Eylül
01	0.280	0.233	0.280	0.414	0.233	0.280	1.87	0.548	0.233	0.233	0.045	0.092
02	0.186	1.18	0.233	0.414	0.186	0.414	1.87	0.548	0.280	0.233	0.045	0.092
03	0.233	1.87	0.233	0.816	0.186	0.548	3.12	0.414	0.414	0.233	0.139	0.092
04	0.233	3.80	0.186	0.414	0.186	0.682	3.46	0.414	0.414	0.233	0.139	0.092
05	0.186	4.88	0.139	0.280	0.186	0.816	2.44	0.414	0.280	0.233	0.139	0.092
06	0.233	2.44	0.139	0.233	0.186	0.682	1.87	0.414	0.233	0.233	0.139	0.092
07	0.186	2.78	0.139	0.233	0.816	0.548	1.64	0.414	0.280	0.233	0.139	0.092
08	0.139	2.10	0.139	0.414	8.56	0.816	1.64	0.414	0.280	0.233	0.139	0.092
09	0.092	1.64	0.139	0.414	4.88	2.10	1.41	0.233	0.414	0.233	0.186	0.092
10	0.092	1.18	0.092	0.414	2.10	1.18	1.18	0.414	0.414	0.233	0.186	0.092
11	0.092	0.816	0.045	0.280	1.87	0.816	1.18	0.414	0.414	0.233	0.186	0.092
12	0.092	0.816	0.045	0.233	3.46	0.682	0.950	0.414	0.414	0.233	0.139	0.092
13	0.139	0.816	0.045	0.233	11.0	0.682	0.950	0.414	0.414	0.139	0.139	0.092
14	0.139	0.548	0.045	0.414	6.40	0.548	0.682	0.414	0.414	0.139	0.139	0.092
15	0.139	0.280	0.045	0.280	3.46	0.682	0.548	0.280	0.414	0.139	0.139	0.092
16	0.139	0.280	0.092	0.280	1.87	0.816	0.548	0.414	0.414	0.139	0.139	0.092
17	0.280	0.280	0.045	0.280	1.18	0.682	0.414	0.682	0.414	0.139	0.139	0.092
18	0.280	0.233	0.029	0.233	0.816	0.816	0.280	0.548	0.414	0.139	0.139	0.092
19	1.18	0.233	5.60	0.233	0.682	0.682	0.280	0.414	0.414	0.139	0.139	0.092
20	0.950	0.233	3.80	1.87	0.548	4.88	0.139	0.414	0.233	0.139	0.139	0.092
21	0.548	2.10	4.88	3.12	0.414	4.16	0.139	0.548	0.233	0.092	0.139	0.092
22	0.280	2.10	2.10	1.87	0.280	2.78	0.139	0.548	0.233	0.092	0.139	0.092
23	0.233	1.18	1.18	1.41	0.280	1.87	0.139	0.414	0.233	0.092	0.139	0.092
24	0.186	0.816	0.950	1.18	0.280	1.64	0.139	0.414	0.233	0.092	0.139	0.092
25	0.092	0.548	0.950	2.10	0.280	1.41	0.139	0.414	0.233	0.092	0.045	0.092
26	0.045	0.548	1.64	4.52	0.280	1.87	0.139	0.414	0.233	0.092	0.045	0.186
27	0.092	0.414	0.950	3.46	0.280	12.5	0.139	0.414	0.233	0.092	0.092	0.139
28	0.092	0.233	0.816	2.10	0.280	7.20	0.139	0.414	0.233	0.092	0.092	0.139
29	0.092	0.233	0.682	1.18	-----	4.16	0.139	0.414	0.233	0.045	0.092	0.139
30	0.139	0.280	0.548	0.682	-----	2.78	0.139	0.280	0.233	0.045	0.092	0.139
31	0.186	-----	0.414	0.414	-----	2.10	-----	0.280	-----	0.045	0.092	-----
Maks.	3.12	8.08	13.7	6.00	25.0	28.8	5.60	0.950	0.414	0.233	0.186	0.816
Min.	0.045	0.092	0.029	0.186	0.045	0.139	0.139	0.139	0.233	0.045	0.045	0.092
Ortalama	0.235	1.17	0.859	0.981	1.83	1.99	0.929	0.425	0.318	0.154	0.124	0.101
LT/SN/Km2	6.71	33.4	24.5	28.0	52.2	57.0	26.5	12.2	9.08	4.40	3.54	2.90
AKIM mm.	18.0	86.6	65.7	75.1	126.	153.	68.8	32.6	23.5	11.8	9.48	7.51
MİL. M3	0.629	3.03	2.30	2.63	4.42	5.34	2.41	1.14	0.823	0.413	0.332	0.263

SU YILI (2006) YILLIK TOPLAM AKIM 23.73 MİLYON M3 678 MM. 21.5 LT/SN/Km2

19. Asi Havzasi

D19A021 AVCILAR S. AVCILAR

YERİ : **İSKENDERUN-ARSUZ BELDESİNİN 15 KM.GÜNEY DOĞUSUNDA AVCILAR KÖYÜNDEDİR.**
35°54'5" Doğu - 36°21'19" Kuzey

YAĞIŞ ALANI : **27,00 km2** **YAKLAŞIK KOT : 100 m**

GÖZLEM SÜRESİ : **01.08.1985 - 30.09.2006**

ORTALAMA AKIMLAR : **Gözlem süresinde 1.032 m3/sn. (18 Yıllık) 2006 Su yılında 1.062 m3/sn.**

ANLIK EN ÇOK VE EN AZ AKIMLAR:

2006 Su yılında anlık ençok akım	:	**10.4**	**m3/sn**	**20.12.2005**
2006 Su yılında anlık enaz akım	:	**0.000**	**m3/sn**	**07.10.2005**
Gözlem süresinde anlık ençok akım	:	**101.**	**m3/sn**	**18.06.1992**
Gözlem süresinde anlık enaz akım	:	**0.000**	**m3/sn**	**01.10.1988**

4. Anahtar Eğrisi (Seviyeler cm olarak)

Seviye	Akım	Seviye	Akım	Seviye	Akım	Seviye	Akım
1	0.000	20	0.019	41	0.631	121	21.5
3	0.000	23	0.025	61	4.0	131	24.6
7	0.004	28	0.047	81	9.2	141	27.7
14	0.011	31	0.089	101	15.3	151	30.9
17	0.014	35	0.160	111	18.4	171	37.7

Akımlar 01 Ekim 2005 'den 30 Eylül 2006' a kadar m3/sn olarak

Gün	Ekim	Kasım	Aralık	Ocak	Şubat	Mart	Nisan	Mayıs	Haziran	Temmuz	Ağustos	Eylül
01	0.057	0.135	0.232	1.05	3.01	1.39	2.09	0.294	0.108	KURU	KURU	KURU
02	0.013	5.46	0.160	1.19	2.79	1.67	2.37	0.257	0.108	KURU	KURU	KURU
03	0.033	4.47	0.135	1.19	2.65	2.09	2.37	0.294	0.094	KURU	KURU	KURU
04	0.089	7.28	0.110	0.913	2.51	2.23	2.09	0.332	0.094	KURU	KURU	KURU
05	0.042	7.28	0.110	0.772	2.51	1.81	1.67	0.332	0.082	KURU	KURU	KURU
06	0.013	4.47	0.100	0.772	3.01	1.27	1.53	0.294	0.082	KURU	KURU	KURU
07	KURU	4.23	0.089	0.772	5.25	1.39	1.39	0.229	0.082	KURU	KURU	KURU
08	KURU	2.62	0.057	0.913	7.63	1.67	1.18	0.173	0.071	KURU	KURU	KURU
09	KURU	1.90	0.047	0.913	5.52	3.01	1.09	0.173	0.054	KURU	KURU	KURU
10	KURU	1.34	0.047	0.913	3.23	2.23	0.928	0.173	0.048	KURU	KURU	KURU
11	KURU	1.05	0.047	0.772	3.67	1.67	0.857	0.156	0.020	KURU	KURU	KURU
12	KURU	0.913	0.042	0.631	4.77	1.67	0.785	0.156	KURU	KURU	KURU	KURU
13	KURU	0.631	0.042	0.631	6.57	1.39	0.857	0.156	KURU	KURU	KURU	KURU
14	KURU	0.376	0.057	0.520	2.79	1.53	0.712	0.156	KURU	KURU	KURU	KURU
15	KURU	0.232	0.448	0.448	1.53	2.79	0.712	0.138	KURU	KURU	KURU	KURU
16	KURU	0.376	2.82	0.448	1.95	2.79	0.646	0.138	KURU	KURU	KURU	KURU
17	0.001	0.304	5.71	0.376	2.37	2.51	0.472	0.332	KURU	KURU	KURU	KURU
18	0.304	0.232	8.38	0.376	2.65	2.65	0.370	1.81	KURU	KURU	KURU	KURU
19	3.98	0.160	7.00	0.520	2.37	6.31	0.370	0.857	KURU	KURU	KURU	KURU
20	2.04	1.19	6.20	3.59	2.37	3.23	0.370	0.580	KURU	KURU	KURU	KURU
21	1.05	5.96	3.40	4.72	2.37	2.65	0.370	0.421	KURU	KURU	KURU	KURU
22	0.520	3.01	3.01	3.01	2.37	2.37	0.370	0.332	KURU	KURU	KURU	KURU
23	0.304	1.90	2.82	2.43	2.09	2.51	0.370	0.294	KURU	KURU	KURU	KURU
24	0.232	1.34	2.62	2.23	1.81	2.79	0.421	0.294	KURU	KURU	KURU	KURU
25	0.160	1.05	2.62	4.47	1.67	3.45	0.421	0.257	KURU	KURU	KURU	KURU
26	0.089	0.913	1.90	7.63	1.67	6.05	0.370	0.173	KURU	KURU	KURU	KURU
27	0.033	0.631	1.62	6.84	1.53	4.11	0.332	0.173	KURU	KURU	KURU	KURU
28	0.024	0.448	1.48	5.25	1.39	2.09	0.332	0.173	KURU	KURU	KURU	KURU
29	0.047	0.304	1.34	4.33	-----	1.39	0.332	0.156	KURU	KURU	KURU	KURU
30	0.448	0.232	1.05	3.89	-----	1.09	0.294	0.123	KURU	KURU	KURU	KURU
31	1.05	-----	1.05	3.45	-----	1.39	-----	0.108	-----	KURU	KURU	-----
Maks.	3.98	8.10	10.4	9.85	9.02	7.91	2.79	2.23	0.123	KURU	KURU	KURU
Min.	KURU	0.135	0.042	0.304	1.27	0.928	0.294	0.108	KURU	KURU	KURU	KURU
Ortalama	0.340	2.01	1.77	2.13	3.00	2.43	0.882	0.308	0.028	KURU	KURU	KURU
LT/SN/Km2	12.6	74.6	65.4	78.8	111.	89.8	32.7	11.4	1.04	0.000	0.000	0.000
AKIM mm.	33.7	193.	175.	211.	269.	241.	84.7	30.5	2.70	0.000	0.000	0.000
MİL. M3	0.910	5.22	4.73	5.70	7.26	6.50	2.29	0.824	0.073	0.000	0.000	0.000

SU YILI (2006) YILLIK TOPLAM AKIM 33.51 MİLYON M3 1241 MM. 39.3 LT/SN/Km2

19. Asi Havzasi

D19A022 BEYKÖY S. BEYKÖY

YERİ : İSKENDERUN-ARSUZ BELDESİNİN 25.KM.SİNDEN SONRA SOLA AYRINAN KÖY YOLUNUN 10.KM.SİNDEKİ BEYKÖYDEDİR.
35°58'20" Doğu - 36°23'57" Kuzey

YAĞIŞ ALANI : 23,00 km2 **YAKLAŞIK KOT** : 100 m

GÖZLEM SÜRESİ : 01.08.1985 - 30.09.2006

ORTALAMA AKIMLAR : Gözlem süresinde 0.289 m3/sn. (21 Yıllık) 2006 Su yılında 0.146 m3/sn.

ANLIK EN ÇOK VE EN AZ AKIMLAR:

2006 Su yılında anlık ençok akım	:	4.53	m3/sn	09.02.2006
2006 Su yılında anlık enaz akım	:	0.000	m3/sn	05.10.2005
Gözlem süresinde anlık ençok akım	:	13.7	m3/sn	09.12.2001
Gözlem süresinde anlık enaz akım	:	0.000	m3/sn	17.07.2005

3. Anahtar Eğrisi (Seviyeler cm olarak)

Seviye	Akım	Seviye	Akım	Seviye	Akım	Seviye	Akım
4	0.000	14	0.160	30	1.0	60	5.2
6	0.017	16	0.230	35	1.5	70	7.1
8	0.036	18	0.300	40	2.1	80	9.5
10	0.066	20	0.400	50	3.5	90	12.1
12	0.110	25	0.680	52	3.8	100	14.7

Akımlar 01 Ekim 2005 'den 30 Eylül 2006' a kadar m3/sn olarak

Gün	Ekim	Kasım	Aralık	Ocak	Şubat	Mart	Nisan	Mayıs	Haziran	Temmuz	Ağustos	Eylül
01	0.026	0.080	0.066	0.190	0.230	0.260	0.260	0.300	0.110	0.026	KURU	0.017
02	0.026	0.130	0.066	0.160	0.230	0.300	0.350	0.260	0.110	0.017	0.010	0.017
03	0.026	0.130	0.066	0.110	0.230	0.300	0.400	0.230	0.130	0.017	0.010	0.017
04	0.026	0.190	0.066	0.080	0.230	0.300	0.350	0.230	0.160	0.017	0.010	0.017
05	0.026	0.230	0.066	0.066	0.230	0.300	0.350	0.190	0.066	0.017	0.010	0.010
06	0.017	0.400	0.066	0.066	0.230	0.260	0.300	0.190	0.050	0.017	0.010	0.017
07	0.026	0.400	0.066	0.066	0.300	0.230	0.300	0.190	0.036	0.017	0.010	0.017
08	0.026	0.350	0.066	0.066	1.14	0.260	0.260	0.230	0.036	0.017	KURU	0.017
09	0.017	0.190	0.066	0.050	0.902	0.350	0.260	0.190	0.036	0.017	0.010	0.017
10	0.017	0.160	0.066	0.066	0.680	0.300	0.260	0.190	0.036	0.010	0.010	0.017
11	0.017	0.110	0.066	0.066	0.624	0.300	0.260	0.190	0.050	0.010	0.010	0.017
12	0.010	0.110	0.066	0.050	0.568	0.260	0.260	0.190	0.066	0.010	0.010	0.017
13	0.017	0.066	0.066	0.050	1.32	0.260	0.260	0.190	0.066	0.010	0.017	0.017
14	0.017	0.066	0.066	0.050	0.828	0.260	0.260	0.160	0.066	0.010	0.017	0.017
15	0.026	0.066	0.066	0.050	0.680	0.260	0.230	0.190	0.080	0.010	0.010	KURU
16	0.026	0.110	0.066	0.066	0.568	0.300	0.230	0.190	0.080	0.010	0.010	KURU
17	0.036	0.110	0.066	0.080	0.456	0.260	0.230	0.190	0.080	0.010	0.010	KURU
18	0.036	0.110	0.066	0.080	0.400	0.260	0.230	0.190	0.066	0.010	0.010	KURU
19	0.066	0.080	0.066	0.080	0.400	0.350	0.230	0.190	0.080	0.010	KURU	KURU
20	0.110	0.066	0.190	0.350	0.400	0.400	0.230	0.160	0.080	0.010	0.010	KURU
21	0.080	0.066	0.190	0.400	0.350	0.400	0.190	0.160	0.066	0.010	0.010	KURU
22	0.050	0.066	0.190	0.260	0.350	0.350	0.190	0.160	0.066	0.017	0.010	KURU
23	0.050	0.066	0.190	0.230	0.350	0.300	0.190	0.110	0.066	0.017	0.026	KURU
24	0.050	0.066	0.190	0.230	0.350	0.300	0.300	0.110	0.050	0.017	0.026	0.010
25	0.050	0.066	0.190	0.300	0.300	0.300	0.260	0.110	0.050	0.010	0.017	0.036
26	0.050	0.066	0.190	0.456	0.300	0.400	0.230	0.110	0.036	0.010	0.017	0.130
27	0.050	0.066	0.190	0.456	0.300	0.400	0.230	0.110	0.036	KURU	0.017	0.050
28	0.066	0.066	0.190	0.400	0.260	0.350	0.230	0.110	0.026	KURU	0.017	0.050
29	0.066	0.066	0.190	0.300	-----	0.300	0.230	0.110	0.026	KURU	0.017	0.066
30	0.080	0.066	0.190	0.260	-----	0.300	0.230	0.130	0.026	KURU	0.017	0.036
31	0.080	-----	0.190	0.260	-----	0.300	-----	0.130	-----	KURU	0.017	-----
Maks.	0.110	0.400	0.190	0.512	4.53	0.624	0.624	0.300	0.160	0.026	0.050	0.230
Min.	KURU	0.066	0.066	0.050	0.190	0.190	0.190	0.066	0.026	KURU	KURU	KURU
Ortalama	0.041	0.127	0.114	0.174	0.472	0.305	0.260	0.174	0.064	0.011	0.012	0.020
LT/SN/Km2	1.78	5.53	4.96	7.57	20.5	13.3	11.3	7.56	2.80	0.495	0.526	0.883
AKIM mm.	4.76	14.3	13.3	20.3	49.6	35.6	29.3	20.2	7.26	1.33	1.41	2.29
MİL. M3	0.109	0.330	0.305	0.466	1.14	0.818	0.673	0.466	0.167	0.030	0.032	0.053

SU YILI (2006) YILLIK TOPLAM AKIM 4.59 MİLYON M3 200 MM. 6.3 LT/SN/Km2

19. Asi Havzasi

D19A023 H.AHMETLİ D. H.AHMETLİ

YERİ : **İSKENDERUN-ARSUZ BELDESİNİN 15.KM.GÜNEYDOĞUSUNDA HACIAHMETLİ KÖYÜNDEDİR.**
35°56'25" Doğu - 36°22'30" Kuzey

YAĞIŞ ALANI : **43,00 km2** **YAKLAŞIK KOT : 80 m**

GÖZLEM SÜRESİ : **01.08.1985 - 30.09.2006**

ORTALAMA AKIMLAR : **Gözlem süresinde 1.056 m3/sn. (20 Yıllık) 2006 Su yılında 0.678 m3/sn.**

ANLIK EN ÇOK VE EN AZ AKIMLAR:

2006 Su yılında anlık ençok akım	**:**	**6.52**	**m3/sn**	**14.02.2006**
2006 Su yılında anlık enaz akım	**:**	**0.062**	**m3/sn**	**20.01.2006**
Gözlem süresinde anlık ençok akım	**:**	**18.5**	**m3/sn**	**29.12.1986**
Gözlem süresinde anlık enaz akım	**:**	**0.000**	**m3/sn**	**02.09.1992**

8. Anahtar Eğrisi (Seviyeler cm olarak)

Seviye	Akım	Seviye	Akım	Seviye	Akım	Seviye	Akım
67	0.065	76	0.361	100	3.1	150	10.8
68	0.106	80	0.712	110	4.3	160	12.4
70	0.152	83	0.976	120	5.7	170	14.0
72	0.197	85	1.2	130	7.4		
75	0.320	90	1.8	140	9.1		

Akımlar 01 Ekim 2005 'den 30 Eylül 2006' a kadar m3/sn olarak

Gün	Ekim	Kasım	Aralık	Ocak	Şubat	Mart	Nisan	Mayıs	Haziran	Temmuz	Ağustos	Eylül
01	0.168	0.253	0.311	0.485	0.921	0.921	1.35	0.834	0.485	0.427	0.253	0.195
02	0.168	0.485	0.311	0.485	0.921	1.27	1.61	0.834	0.485	0.427	0.253	0.195
03	0.195	0.427	0.253	0.485	0.921	1.44	1.61	0.776	0.485	0.427	0.253	0.195
04	0.195	0.776	0.253	0.485	0.921	1.44	1.44	0.776	0.485	0.311	0.311	0.195
05	0.195	1.01	0.253	0.485	0.921	1.27	1.35	0.776	0.485	0.485	0.311	0.195
06	0.195	0.602	0.253	0.485	1.09	1.27	1.27	0.776	0.485	0.369	0.253	0.195
07	0.168	0.718	0.253	0.485	1.79	1.27	1.27	0.776	0.485	0.369	0.253	0.195
08	0.168	0.602	0.253	0.544	4.43	1.35	1.18	0.718	0.485	0.369	0.253	0.195
09	0.168	0.485	0.253	0.544	3.55	1.70	1.18	0.718	0.485	0.369	0.253	0.195
10	0.168	0.427	0.253	0.427	2.89	1.35	1.09	0.718	0.485	0.369	0.253	0.195
11	0.168	0.369	0.195	0.427	2.78	1.27	1.01	0.718	0.485	0.369	0.253	0.195
12	0.168	0.369	0.195	0.427	3.22	1.27	1.01	0.718	0.485	0.369	0.253	0.195
13	0.168	0.311	0.195	0.427	4.65	1.27	1.01	0.718	0.485	0.253	0.253	0.195
14	0.168	0.311	0.195	0.427	3.33	1.27	1.01	0.660	0.427	0.253	0.253	0.195
15	0.168	0.311	0.195	0.427	2.67	1.35	0.921	0.660	0.427	0.253	0.195	0.195
16	0.168	0.311	0.195	0.427	2.12	1.35	0.921	0.660	0.427	0.253	0.195	0.195
17	0.253	0.311	0.195	0.369	1.79	1.27	0.834	0.660	0.427	0.253	0.195	0.195
18	0.195	0.253	1.09	0.369	1.53	1.35	0.834	0.660	0.427	0.253	0.195	0.195
19	0.427	0.253	1.01	0.369	1.35	2.45	0.718	0.660	0.427	0.253	0.195	0.195
20	0.311	0.311	2.01	1.09	1.35	2.01	0.776	0.660	0.427	0.253	0.195	0.195
21	0.195	0.834	1.09	1.18	1.27	1.79	0.776	0.602	0.427	0.253	0.195	0.195
22	0.195	0.544	0.834	0.921	1.27	1.61	1.01	0.602	0.427	0.253	0.195	0.195
23	0.195	0.427	0.921	0.834	1.27	1.53	1.01	0.544	0.427	0.253	0.195	0.195
24	0.195	0.427	0.921	0.776	1.18	1.44	0.834	0.544	0.427	0.253	0.195	0.195
25	0.168	0.427	1.09	1.09	1.18	1.61	0.834	0.544	0.427	0.253	0.195	0.427
26	0.168	0.369	0.834	1.53	1.27	3.00	0.834	0.544	0.427	0.253	0.195	0.369
27	0.168	0.311	0.776	1.53	1.27	2.45	0.834	0.544	0.427	0.253	0.195	0.311
28	0.168	0.311	0.718	1.27	1.18	1.90	0.834	0.544	0.427	0.253	0.195	0.253
29	0.168	0.311	0.660	1.09	-----	1.70	0.834	0.544	0.427	0.253	0.195	0.253
30	0.195	0.311	0.602	1.09	-----	1.53	0.834	0.544	0.427	0.253	0.195	0.253
31	0.253	-----	0.602	0.921	-----	1.44	-----	0.485	-----	0.253	0.195	-----
Maks.	0.602	2.01	4.10	2.89	6.52	5.31	2.12	1.01	0.485	0.544	0.369	0.602
Min.	0.168	0.168	0.168	0.062	0.776	0.369	0.660	0.485	0.253	0.253	0.195	0.195
Ortalama	0.195	0.439	0.554	0.706	1.89	1.55	1.03	0.662	0.452	0.305	0.225	0.218
LT/SN/Km2	4.54	10.2	12.9	16.4	44.0	36.1	24.1	15.4	10.5	7.10	5.23	5.07
AKIM mm.	12.2	26.5	34.5	44.0	107.	96.7	62.3	41.2	27.3	19.0	14.0	13.2
MİL. M3	0.523	1.14	1.48	1.89	4.58	4.16	2.68	1.77	1.17	0.818	0.602	0.566

SU YILI (2006) YILLIK TOPLAM AKIM 21.38 MİLYON M3 497 MM. 15.8 LT/SN/Km2

19. Asi Havzasi

D19A026 KÜÇÜK ASİ N. HASANLI KÖP.

YERİ : **ANTAKYA-İSKENDERUN YOLUNUN 10.KM SİNDEN SAĞA AYRILAN HASANLI KÖYÜNE GİDEN YOLUN KÜÇÜK ASİ NEHRİNİ KESTİĞİ KÖPRÜDEDİR.**
36°12'29" Doğu - 36°16'22" Kuzey

YAĞIŞ ALANI : **6244,40 km2** **YAKLAŞIK KOT : 75 m**

GÖZLEM SÜRESİ : **15.05.1987 - 30.09.2006**

ORTALAMA AKIMLAR : **Gözlem süresinde 24.133 m3/sn. (14 Yıllık) 2006 Su yılında 12.462 m3/sn.**

ANLIK EN ÇOK VE EN AZ AKIMLAR:

2006 Su yılında anlık ençok akım	:	**104.**	**m3/sn**	**13.02.2006**
2006 Su yılında anlık enaz akım	:	**0.000**	**m3/sn**	**20.05.2006**
Gözlem süresinde anlık ençok akım	:	**365.**	**m3/sn**	**16.02.1994**
Gözlem süresinde anlık enaz akım	:	**0.000**	**m3/sn**	**09.06.1989**

6. Anahtar Eğrisi (Seviyeler cm olarak)

Seviye	Akım	Seviye	Akım	Seviye	Akım	Seviye	Akım
1	0.100	65	11.5	121	32.0	321	160.
21	2.3	73	14.0	161	48.0	361	190.
41	5.8	81	16.5	201	70.0	401	230.
49	7.4	89	19.0	241	98.0	441	270.
57	9.4	97	22.0	281	125.	701	580.

Akımlar 01 Ekim 2005 'den 30 Eylül 2006' a kadar m3/sn olarak

Gün	Ekim	Kasım	Aralık	Ocak	Şubat	Mart	Nisan	Mayıs	Haziran	Temmuz	Ağustos	Eylül
01	3.42	11.2	10.1	12.7	35.8	17.9	15.8	5.28	KURU	KURU	KURU	KURU
02	4.31	11.4	10.5	11.7	30.8	16.0	17.1	5.16	KURU	KURU	KURU	KURU
03	4.80	11.9	9.99	11.4	30.2	17.5	20.5	5.16	KURU	KURU	KURU	KURU
04	5.28	12.1	9.99	11.2	26.1	16.8	23.4	5.16	KURU	KURU	KURU	KURU
05	5.52	12.5	9.99	10.8	23.9	16.0	30.2	5.16	KURU	KURU	KURU	KURU
06	5.64	12.3	9.83	10.7	23.4	16.0	35.4	5.04	KURU	KURU	KURU	KURU
07	5.64	12.7	9.83	10.7	25.8	15.4	35.8	4.92	KURU	KURU	KURU	KURU
08	6.40	13.6	9.99	10.7	49.3	13.4	33.6	4.80	KURU	KURU	KURU	KURU
09	9.36	12.7	9.83	10.8	75.1	11.4	31.1	4.80	KURU	KURU	KURU	KURU
10	10.3	12.1	9.83	10.7	69.9	15.0	28.1	4.70	KURU	KURU	KURU	KURU
11	4.40	12.3	9.83	10.8	77.8	16.8	25.3	4.70	KURU	KURU	KURU	KURU
12	4.60	12.1	9.52	11.0	80.0	20.5	22.3	4.60	KURU	KURU	KURU	KURU
13	4.80	11.4	9.36	11.7	94.2	23.6	19.3	4.60	KURU	KURU	KURU	KURU
14	5.04	11.2	9.05	13.1	98.2	23.4	16.0	4.60	KURU	KURU	KURU	4.80
15	5.28	11.0	8.74	16.2	88.0	21.8	13.4	4.60	KURU	KURU	KURU	12.7
16	5.52	11.4	9.21	20.0	78.9	20.0	14.0	4.60	KURU	KURU	KURU	23.1
17	6.26	11.2	9.52	20.3	67.0	18.6	17.1	4.50	KURU	KURU	KURU	29.9
18	6.53	9.83	11.7	17.1	62.4	17.9	17.9	4.80	KURU	KURU	KURU	34.8
19	7.06	8.90	12.5	16.0	57.3	21.8	14.0	0.597	KURU	KURU	KURU	41.9
20	7.32	8.74	12.9	21.8	49.3	30.8	11.2	KURU	KURU	KURU	KURU	14.4
21	7.46	9.99	13.6	24.7	38.0	29.3	8.74	KURU	KURU	KURU	KURU	9.21
22	7.75	11.4	13.1	32.9	34.2	27.3	8.74	KURU	KURU	KURU	KURU	5.88
23	8.03	12.1	11.9	43.9	31.7	25.0	8.60	KURU	KURU	KURU	KURU	8.03
24	8.31	11.7	13.4	42.3	29.0	21.5	6.79	KURU	KURU	KURU	KURU	6.66
25	8.60	10.8	16.2	38.7	26.1	20.3	6.13	KURU	KURU	KURU	KURU	6.66
26	9.99	10.5	16.2	45.9	24.2	32.6	5.16	KURU	KURU	KURU	KURU	7.46
27	9.68	10.5	14.8	61.9	22.8	27.8	5.04	KURU	KURU	KURU	KURU	9.05
28	9.83	10.1	15.0	63.3	21.5	24.5	5.28	KURU	KURU	KURU	KURU	9.05
29	9.68	9.83	15.2	59.6	-----	23.1	5.52	KURU	KURU	KURU	KURU	11.4
30	9.83	9.99	15.8	53.7	-----	20.5	5.28	KURU	KURU	KURU	KURU	11.6
31	10.8	-----	14.4	43.5	-----	17.5	-----	KURU	-----	KURU	KURU	-----
Maks.	11.0	13.8	16.2	67.9	104.	37.7	36.7	6.00	KURU	KURU	KURU	50.1
Min.	2.68	8.74	8.74	10.7	20.5	11.2	5.04	KURU	KURU	KURU	KURU	KURU
Ortalama	7.01	11.2	11.7	25.2	49.0	20.6	16.9	2.83	KURU	KURU	KURU	8.22
LT/SN/Km2	1.12	1.80	1.87	4.03	7.84	3.31	2.71	0.453	0.000	0.000	0.000	1.32
AKIM mm.	3.01	4.67	5.01	10.8	19.0	8.86	7.01	1.21	0.000	0.000	0.000	3.41
MİL. M3	18.8	29.2	31.3	67.4	118.	55.3	43.8	7.58	0.000	0.000	0.000	21.3

SU YILI (2006) YILLIK TOPLAM AKIM 392.68 MİLYON M3 63 MM. 2.0 LT/SN/Km2

19. Asi Havzasi

D19A027 KARASU N. ARPAHAN

YERİ : **ANTAKYA-İSKENDERUN KARAYOLUNUN 20.KM.SİNDEN SOLA AYRILAN ARPAHAN KÖY YOLUNUN KARASUYU KESTİĞİ KÖPRÜDEDİR.**
36°15'15" Doğu - 36°20'3" Kuzey

YAĞIŞ ALANI : **6244,40 km2** **YAKLAŞIK KOT : 78 m**

GÖZLEM SÜRESİ : **14.05.1987 - 30.09.2006**

ORTALAMA AKIMLAR : **Gözlem süresinde 8.356 m3/sn. (11 Yıllık) 2006 Su yılında 6.223 m3/sn.**

ANLIK EN ÇOK VE EN AZ AKIMLAR:

2006 Su yılında anlık ençok akım	:	**50.0**	**m3/sn**	**14.02.2006**
2006 Su yılında anlık enaz akım	:	**0.000**	**m3/sn**	**30.06.2006**
Gözlem süresinde anlık ençok akım	:	**110.**	**m3/sn**	**08.05.2001**
Gözlem süresinde anlık enaz akım	:	**0.000**	**m3/sn**	**31.05.1989**

Akımlar 01 Ekim 2005 'den 30 Eylül 2006' a kadar m3/sn olarak

Gün	Ekim	Kasım	Aralık	Ocak	Şubat	Mart	Nisan	Mayıs	Haziran	Temmuz	Ağustos	Eylül
01	1.64	4.34	5.72	6.52	15.2	10.4	7.00	2.36	2.36	KURU	KURU	KURU
02	1.92	4.90	5.40	6.04	13.1	9.84	7.96	2.52	0.940	KURU	KURU	KURU
03	2.06	5.10	5.40	5.72	14.3	9.76	11.5	2.36	KURU	KURU	KURU	KURU
04	2.06	5.00	5.40	5.72	12.2	9.04	11.6	2.52	KURU	KURU	KURU	KURU
05	2.06	5.72	5.30	5.56	11.1	8.62	14.3	2.52	KURU	KURU	KURU	KURU
06	2.06	5.56	5.30	5.30	11.9	7.96	20.4	2.68	KURU	KURU	KURU	KURU
07	2.20	5.40	5.20	5.30	15.6	7.36	21.0	2.52	KURU	KURU	KURU	KURU
08	2.20	6.20	5.20	5.30	31.2	7.12	19.9	2.68	KURU	KURU	KURU	KURU
09	1.92	5.72	5.10	5.40	42.8	7.96	18.4	2.84	KURU	KURU	KURU	KURU
10	1.78	5.56	5.56	5.40	38.4	11.7	16.6	2.36	KURU	KURU	KURU	KURU
11	1.78	5.00	5.56	5.30	40.0	11.3	14.5	2.84	KURU	KURU	KURU	KURU
12	1.92	5.10	5.40	5.30	40.0	10.3	11.7	3.16	KURU	KURU	KURU	KURU
13	1.92	5.00	5.40	5.30	45.6	10.9	9.31	3.32	KURU	KURU	KURU	KURU
14	2.06	5.00	4.76	5.30	48.4	10.5	8.16	3.32	KURU	KURU	KURU	KURU
15	2.32	4.90	4.34	5.40	44.4	10.1	7.84	3.32	KURU	KURU	KURU	KURU
16	2.32	4.90	5.00	5.56	40.2	10.0	7.84	3.00	KURU	KURU	KURU	KURU
17	2.68	5.00	5.10	5.72	34.0	9.92	12.9	3.16	KURU	KURU	KURU	KURU
18	2.80	4.90	8.76	5.72	31.2	9.92	12.8	4.34	KURU	KURU	KURU	KURU
19	2.80	4.90	8.62	5.72	28.7	11.1	9.14	4.34	KURU	KURU	KURU	1.36
20	5.56	4.90	8.76	9.04	24.6	19.2	7.52	4.34	KURU	KURU	KURU	1.36
21	5.10	7.24	9.18	12.6	19.2	16.2	6.72	4.16	KURU	KURU	KURU	1.36
22	4.76	7.96	8.34	13.7	17.1	14.0	7.20	4.16	KURU	KURU	KURU	1.36
23	4.34	7.48	7.48	17.6	15.6	12.6	6.40	4.16	KURU	KURU	KURU	1.64
24	4.34	6.84	7.84	17.3	14.3	10.2	5.92	4.34	KURU	KURU	KURU	1.64
25	3.78	5.40	10.7	16.1	13.2	9.76	5.06	4.16	KURU	KURU	KURU	2.06
26	3.50	5.56	10.2	20.1	12.5	14.4	3.98	3.98	KURU	KURU	KURU	5.24
27	3.36	5.56	8.76	28.9	11.9	15.9	3.00	3.80	KURU	KURU	KURU	4.34
28	3.64	5.56	7.84	28.3	11.3	13.2	3.16	3.48	KURU	KURU	KURU	3.64
29	3.64	5.40	7.60	26.0	-----	11.8	4.16	3.16	KURU	KURU	KURU	3.64
30	3.50	5.56	7.48	22.8	-----	9.92	3.16	2.84	KURU	KURU	KURU	3.32
31	3.92	-----	7.00	18.8	-----	7.72	-----	2.52	-----	KURU	KURU	-----
Maks.	10.3	8.34	10.9	32.2	50.0	20.4	21.8	4.88	3.48	KURU	KURU	17.0
Min.	1.40	4.06	3.50	5.30	10.7	7.12	2.20	1.92	KURU	KURU	KURU	KURU
Ortalama	2.90	5.52	6.70	10.9	24.9	10.9	9.97	3.27	0.110	KURU	KURU	1.03
LT/SN/Km2	0.465	0.884	1.07	1.74	3.99	1.75	1.60	0.523	0.018	0.000	0.000	0.165
AKIM mm.	1.24	2.29	2.87	4.66	9.66	4.69	4.14	1.40	0.046	0.000	0.000	0.428
MİL. M3	7.77	14.3	17.9	29.1	60.3	29.3	25.8	8.75	0.285	0.000	0.000	2.67

SU YILI (2006) YILLIK TOPLAM AKIM 196.18 MİLYON M3 31 MM. 1.0 LT/SN/Km2

19. Asi Havzasi

D19A028 BEYAZ Ç. ALAKENT

YERİ : **HATAY İLİ ALTINÖZÜ İLÇESİ ATAKENT KÖYÜ YAKINLARINDAKİ KÖPRÜDEDİR.**
36°18'35" Doğu - 36°7'45" Kuzey

YAĞIŞ ALANI : **193,20 km2** **YAKLAŞIK KOT : 195 m**

GÖZLEM SÜRESİ : **01.02.1993 - 30.09.2006**

ORTALAMA AKIMLAR : **Gözlem süresinde 0.972 m3/sn. (14 Yıllık) 2006 Su yılında 0.486 m3/sn.**

ANLIK EN ÇOK VE EN AZ AKIMLAR:

2006 Su yılında anlık ençok akım	**:**	**9.24**	**m3/sn**	**19.03.2006**
2006 Su yılında anlık enaz akım	**:**	**0.000**	**m3/sn**	**02.08.2006**
Gözlem süresinde anlık ençok akım	**:**	**80.8**	**m3/sn**	**15.02.1994**
Gözlem süresinde anlık enaz akım	**:**	**0.000**	**m3/sn**	**02.08.2006**

1. Anahtar Eğrisi (Seviyeler cm olarak)

Seviye	Akım	Seviye	Akım	Seviye	Akım	Seviye	Akım
10	0.024	56	3.4	170	28.0	380	73.0
15	0.050	65	5.0	220	40.0	420	80.0
25	0.180	75	7.5	260	48.0	440	84.0
35	0.650	90	10.5	300	57.0	460	87.0
44	1.5	120	17.0	340	65.0	480	91.0

Akımlar 01 Ekim 2005 'den 30 Eylül 2006' a kadar m3/sn olarak

Gün	Ekim	Kasım	Aralık	Ocak	Şubat	Mart	Nisan	Mayıs	Haziran	Temmuz	Ağustos	Eylül
01	0.219	0.263	0.219	0.219	0.707	0.880	1.02	0.629	0.161	0.122	0.066	0.031
02	0.219	0.263	0.219	0.219	0.707	0.880	1.82	0.590	0.190	0.058	0.075	0.058
03	0.219	0.263	0.219	0.219	0.707	0.880	1.76	0.590	0.161	0.075	0.075	0.049
04	0.219	0.307	0.219	0.219	0.707	0.880	1.51	0.590	0.161	0.075	0.066	0.049
05	0.219	0.219	0.219	0.219	0.668	0.880	1.69	0.551	0.161	0.075	0.075	0.058
06	0.219	0.190	0.219	0.219	0.629	0.880	1.38	0.551	0.161	0.075	0.075	0.066
07	0.219	0.190	0.219	0.219	0.928	0.880	1.32	0.512	0.083	0.083	0.075	0.049
08	0.219	0.190	0.219	0.219	2.50	0.880	1.26	0.473	0.190	0.066	0.066	0.058
09	0.219	0.190	0.219	0.219	3.64	1.12	1.21	0.473	0.161	0.066	0.075	0.066
10	0.219	0.161	0.219	0.219	2.92	1.45	1.17	0.473	0.161	0.066	0.075	0.066
11	0.219	0.161	0.219	0.219	1.82	0.928	1.07	0.434	0.161	0.075	0.075	0.049
12	0.219	0.161	0.219	0.307	1.57	0.880	1.07	0.395	0.161	0.075	0.075	0.058
13	0.219	0.161	0.219	0.668	2.92	0.880	1.07	0.351	0.161	0.040	0.075	0.049
14	0.219	0.161	0.219	0.434	2.58	0.880	1.07	0.395	0.122	0.058	0.049	0.058
15	0.219	0.161	0.219	0.307	3.83	1.02	1.02	0.307	0.161	0.049	0.040	0.058
16	0.219	0.190	0.263	0.263	2.43	0.928	0.975	0.351	0.122	0.058	0.049	0.058
17	0.307	0.190	0.307	0.263	1.82	0.975	0.975	0.395	0.122	0.058	0.058	0.066
18	0.307	0.190	0.263	0.351	1.57	1.02	0.928	0.395	0.122	0.058	0.049	0.066
19	0.307	0.190	0.219	0.395	1.45	4.11	0.880	0.307	0.122	0.049	0.049	0.058
20	0.307	0.219	0.351	1.88	1.38	2.84	0.880	0.307	0.161	0.058	0.066	0.058
21	0.307	0.473	0.219	1.02	1.26	1.63	0.880	0.307	0.161	0.049	0.040	0.066
22	0.307	0.219	0.219	0.668	1.17	1.38	0.880	0.307	0.161	0.058	0.049	0.075
23	0.307	0.219	0.263	0.746	1.12	1.21	0.833	0.307	0.161	0.058	0.031	0.058
24	0.307	0.190	0.351	0.746	1.07	1.17	0.833	0.307	0.122	0.058	0.031	0.058
25	0.307	0.190	0.351	0.975	1.02	1.17	0.833	0.263	0.122	0.040	0.049	0.075
26	0.307	0.219	0.307	2.19	0.975	1.63	0.833	0.219	0.122	0.049	0.049	0.075
27	0.307	0.219	0.219	2.35	0.928	1.26	0.785	0.219	0.122	0.049	0.049	0.075
28	0.307	0.219	0.219	1.26	0.880	1.17	0.746	0.219	0.122	0.049	0.058	0.075
29	0.307	0.219	0.219	0.928	-----	1.07	0.707	0.219	0.122	0.040	0.058	0.066
30	0.473	0.219	0.219	0.833	-----	1.02	0.668	0.190	0.122	0.040	0.058	0.066
31	0.351	-----	0.219	0.785	-----	1.02	-----	0.190	-----	0.066	0.049	-----
Maks.	0.512	0.629	0.395	4.30	4.59	9.24	2.04	0.707	0.190	0.190	0.075	0.075
Min.	0.190	0.161	0.219	0.219	0.629	0.880	0.629	0.161	0.066	0.031	KURU	KURU
Ortalama	0.268	0.214	0.242	0.638	1.57	1.22	1.07	0.381	0.145	0.061	0.059	0.061
LT/SN/Km2	1.39	1.11	1.25	3.30	8.12	6.31	5.53	1.97	0.749	0.316	0.305	0.313
AKIM mm.	3.72	2.86	3.35	8.84	19.6	16.9	14.3	5.28	1.94	0.847	0.818	0.813
MİL. M3	0.719	0.553	0.647	1.71	3.79	3.27	2.77	1.02	0.375	0.164	0.158	0.157

SU YILI (2006) YILLIK TOPLAM AKIM 15.33 MİLYON M3 79 MM. 2.5 LT/SN/Km2

19. Asi Havzasi

D19A029 BÜYÜK KARAÇAY YAYLICA

YERİ : **ANTAKYA-SAMANDAĞ KARAYOLUNUN 15.KM.DEN SAĞA AYRILAN BATIAYAZ YOLUNUN B.KARAÇAYI KESTİĞİ KÖPRÜNÜN 200 M. MANSABINDADIR.**
36°0'54" Doğu - 36°9'39" Kuzey

YAĞIŞ ALANI : **107,80 km2** **YAKLAŞIK KOT : 139 m**

GÖZLEM SÜRESİ : **10.09.1992 - 30.09.2006**

ORTALAMA AKIMLAR : **Gözlem süresinde 2.828 m3/sn. (12 Yıllık) 2006 Su yılında 2.436 m3/sn.**

ANLIK EN ÇOK VE EN AZ AKIMLAR:

2006 Su yılında anlık ençok akım	:	**57.0**	**m3/sn**	**26.03.2006**
2006 Su yılında anlık enaz akım	:	**0.045**	**m3/sn**	**29.08.2006**
Gözlem süresinde anlık ençok akım	:	**570.**	**m3/sn**	**21.05.1998**
Gözlem süresinde anlık enaz akım	:	**0.040**	**m3/sn**	**21.10.1993**

Akımlar 01 Ekim 2005 'den 30 Eylül 2006' a kadar m3/sn olarak

Gün	Ekim	Kasım	Aralık	Ocak	Şubat	Mart	Nisan	Mayıs	Haziran	Temmuz	Ağustos	Eylül
01	0.787	0.483	0.686	1.70	3.57	2.46	6.07	1.50	0.585	0.483	0.180	0.062
02	0.483	1.50	0.686	1.60	3.20	2.46	6.95	1.50	0.686	0.281	0.180	0.062
03	0.483	1.19	0.585	1.50	3.01	2.27	6.07	1.39	0.686	0.180	0.078	0.045
04	0.382	4.04	0.585	1.39	2.64	2.27	9.60	1.39	0.382	0.180	0.078	0.062
05	0.281	4.91	0.585	1.29	2.64	2.09	6.95	1.39	0.382	0.382	0.062	0.045
06	0.281	1.90	0.483	1.29	2.46	1.90	6.36	1.29	0.281	0.382	0.180	0.045
07	0.281	2.27	0.483	1.19	3.75	1.90	5.78	1.29	0.281	1.29	0.180	0.045
08	0.062	1.60	0.483	1.50	14.9	1.90	5.20	1.19	0.382	0.787	0.180	0.045
09	0.062	1.29	0.483	1.39	16.6	3.38	4.62	1.19	0.382	0.281	0.180	0.045
10	0.180	1.09	0.483	1.29	12.9	3.20	4.04	1.09	0.180	0.078	0.281	0.045
11	0.180	0.989	0.483	1.19	11.1	2.64	3.75	0.989	0.180	0.180	0.281	0.062
12	0.180	0.888	0.382	1.19	12.3	2.46	3.38	0.989	0.180	0.382	0.078	0.045
13	0.180	0.888	0.382	1.29	23.1	2.46	3.20	0.888	0.180	0.483	0.078	0.045
14	0.180	0.888	0.382	1.19	16.2	2.27	3.01	0.787	0.686	0.585	0.180	0.045
15	0.180	0.888	0.382	1.19	14.6	3.20	2.83	0.787	1.90	0.585	0.180	0.062
16	0.180	0.888	0.585	1.19	10.8	3.01	2.64	0.787	2.09	0.382	0.180	0.045
17	0.180	0.787	0.989	1.09	8.72	4.04	2.46	0.888	2.09	0.078	0.078	0.062
18	0.180	0.787	5.20	2.09	7.24	5.20	2.27	7.54	1.80	0.281	0.062	0.045
19	1.50	0.686	5.78	1.80	6.07	31.8	2.09	1.90	1.50	0.281	0.045	0.045
20	1.19	1.19	14.3	10.8	5.20	15.6	2.09	1.29	1.39	0.281	0.078	0.045
21	0.787	6.65	4.91	6.07	4.62	10.2	1.90	0.989	1.39	0.585	0.180	0.062
22	0.585	1.70	3.01	3.57	4.04	8.13	1.80	0.888	1.60	0.989	0.281	0.382
23	0.483	1.29	5.49	3.20	3.57	6.95	1.80	0.787	1.39	1.09	0.078	1.09
24	0.382	1.09	7.54	6.07	3.38	6.07	2.27	0.686	0.787	0.989	0.062	0.585
25	0.382	0.989	8.42	13.9	3.20	8.42	1.90	0.686	0.483	0.686	0.045	3.40
26	0.281	0.888	4.91	19.8	3.01	30.2	1.80	0.585	0.281	0.585	0.062	0.730
27	0.281	0.787	3.38	13.6	2.83	15.6	1.70	0.686	0.281	0.585	0.062	0.410
28	0.281	0.787	2.83	8.72	2.64	11.4	1.70	0.787	0.281	0.585	0.062	0.323
29	0.281	0.787	2.27	6.36	-----	9.31	1.60	0.787	0.281	0.787	0.045	0.279
30	0.686	0.686	1.90	5.20	-----	8.13	1.60	0.787	0.686	0.585	0.045	0.255
31	0.585	-----	1.80	4.04	-----	6.95	-----	0.686	-----	0.180	0.045	-----
Maks.	4.04	18.6	41.8	32.4	40.7	57.0	24.1	17.3	2.46	1.70	0.483	24.7
Min.	0.062	0.483	0.382	1.09	2.46	1.90	1.60	0.483	0.078	0.078	0.045	0.045
Ortalama	0.401	1.49	2.61	4.12	7.44	7.03	3.58	1.24	0.789	0.500	0.122	0.284
LT/SN/Km2	3.72	13.9	24.2	38.2	69.0	65.2	33.2	11.5	7.32	4.63	1.13	2.63
AKIM mm.	9.96	35.9	64.8	102.	167.	175.	86.1	30.8	19.0	12.4	3.03	6.83
MİL. M3	1.07	3.87	6.99	11.0	18.0	18.8	9.28	3.32	2.05	1.34	0.327	0.736

SU YILI (2006) YILLIK TOPLAM AKIM 76.78 MİLYON M3 712 MM. 22.6 LT/SN/Km2

19. Asi Havzasi

D19A030 ASİ N. EŞREFİYE KARAKOLU

YERİ : **TÜRKİYE - SURİYE SINIRINDAKİ EŞREFİYE KARAKOLU YAKININDAKİ KÖPRÜDEDİR.**
36°23'18" Doğu - 36°13'17" Kuzey

YAĞIŞ ALANI : **16120,00 km2** **YAKLAŞIK KOT : 95 m**

GÖZLEM SÜRESİ : **01.10.1997 - 30.09.2006**

ORTALAMA AKIMLAR : **Gözlem süresinde 17.496 m3/sn. (9 Yıllık) 2006 Su yılında 15.880 m3/sn.**

ANLIK EN ÇOK VE EN AZ AKIMLAR:

2006 Su yılında anlık ençok akım	**:**	**83.9**	**m3/sn**	**29.01.2006**
2006 Su yılında anlık enaz akım	**:**	**0.000**	**m3/sn**	**26.05.2006**
Gözlem süresinde anlık ençok akım	**:**	**170.**	**m3/sn**	**25.02.2003**
Gözlem süresinde anlık enaz akım	**:**	**0.000**	**m3/sn**	**15.07.2005**

Akımlar 01 Ekim 2005 'den 30 Eylül 2006' a kadar m3/sn olarak

Gün	Ekim	Kasım	Aralık	Ocak	Şubat	Mart	Nisan	Mayıs	Haziran	Temmuz	Ağustos	Eylül
01	10.4	15.2	8.21	14.3	54.7	22.2	29.2	10.1	3.51	1.52	1.67	0.905
02	11.1	16.5	8.21	13.8	49.2	28.5	29.4	10.6	3.75	1.17	1.98	1.04
03	11.4	16.9	8.21	13.6	45.2	29.6	34.8	9.94	2.76	1.52	0.905	1.59
04	11.5	17.0	8.21	13.1	42.7	27.4	43.2	9.46	2.68	1.67	1.23	1.45
05	12.2	16.5	8.21	12.8	40.9	29.4	53.9	8.50	2.76	2.06	0.905	0.421
06	12.3	17.0	8.21	12.7	39.2	29.8	57.6	7.49	2.68	1.90	1.52	0.502
07	13.6	18.2	8.21	12.3	32.8	27.0	53.9	4.49	2.83	1.90	3.63	0.542
08	22.4	17.7	8.21	12.3	36.8	15.7	49.6	3.14	3.87	1.82	3.14	0.542
09	26.1	15.9	8.21	12.5	38.5	15.5	46.3	2.91	4.49	1.67	3.14	0.905
10	25.0	17.4	8.21	12.7	43.4	21.5	43.4	2.68	5.42	1.23	4.12	1.98
11	21.5	17.0	8.50	13.6	56.5	30.9	41.2	2.06	4.12	0.905	3.63	3.14
12	16.4	16.0	8.50	14.7	65.5	40.0	39.0	1.98	4.62	1.10	3.26	3.14
13	13.1	15.5	8.50	16.5	63.4	41.2	34.5	1.98	5.42	1.23	3.38	3.14
14	12.5	14.8	8.50	23.7	60.8	40.0	22.0	1.67	4.24	1.67	2.68	3.14
15	11.9	14.0	8.50	33.3	63.0	36.3	24.6	1.90	3.75	1.17	0.623	3.14
16	12.0	13.8	8.50	37.0	64.1	32.1	28.3	1.52	3.51	0.736	0.679	3.14
17	12.5	10.7	8.50	31.1	65.5	29.4	29.2	1.37	2.83	0.970	0.849	3.14
18	12.7	7.64	8.82	29.8	62.6	30.7	28.5	1.52	2.06	1.37	1.67	3.26
19	14.0	7.06	9.30	29.2	57.2	32.3	23.7	1.37	1.82	1.30	1.30	3.99
20	15.2	7.20	9.62	36.8	52.1	34.5	13.8	1.17	1.75	1.67	0.970	5.82
21	15.7	7.49	9.78	35.3	48.1	38.5	14.5	1.23	1.45	1.45	0.970	6.23
22	15.2	10.3	9.78	30.2	45.6	37.3	14.3	0.849	1.52	1.10	1.17	7.49
23	14.8	12.3	9.78	29.8	43.4	35.5	7.20	1.17	1.75	1.04	1.17	10.9
24	14.5	11.4	9.94	64.1	40.7	34.1	4.24	0.849	1.59	1.10	0.792	10.3
25	14.3	10.9	10.4	62.3	39.0	31.1	3.99	0.583	1.37	1.59	0.970	10.3
26	14.2	10.4	12.0	62.6	37.7	28.9	4.76	0.461	1.23	1.17	1.04	11.9
27	14.0	10.3	14.5	73.2	36.5	30.2	9.14	0.583	1.45	0.970	1.52	13.5
28	13.6	9.30	17.2	81.4	30.9	33.8	7.92	1.17	1.52	1.10	1.10	18.6
29	13.3	8.50	21.1	82.7	-----	33.8	8.21	0.623	1.59	1.10	1.52	22.0
30	14.7	8.36	18.9	74.6	-----	31.6	10.1	0.461	1.59	1.10	1.67	16.5
31	15.0	-----	15.5	63.0	-----	29.8	-----	3.26	-----	1.10	1.17	-----
Maks.	26.3	18.6	21.8	83.9	66.6	41.7	59.0	12.2	6.65	2.68	5.55	23.3
Min.	8.98	7.06	8.21	12.0	25.0	13.1	3.75	KURU	1.10	KURU	0.384	0.384
Ortalama	14.7	13.0	10.3	34.0	48.4	30.9	27.0	3.13	2.80	1.34	1.75	5.75
LT/SN/Km2	0.915	0.809	0.637	2.11	3.00	1.92	1.68	0.194	0.174	0.083	0.109	0.357
AKIM mm.	2.45	2.10	1.71	5.65	7.27	5.14	4.34	0.520	0.450	0.222	0.291	0.925
MİL. M3	39.5	33.8	27.5	91.2	117.	82.8	70.0	8.39	7.25	3.58	4.70	14.9

SU YILI (2006) YILLIK TOPLAM AKIM 500.62 MİLYON M3 31 MM. 1.0 LT/SN/Km2

19. Asi Havzasi

D19A031 KARASU N. KALETEPE

YERİ : **TÜRKİYE-SURİYE SINIRINDA KALETEPE KÖYÜ YAKININDAKİ KALETEPE KÖYÜNDEKİ KARASU NEHRİ KÖPRÜSÜNDEDİR.**
36°34'25" Doğu - 36°39'38" Kuzey

YAĞIŞ ALANI : **1042,60 km2** **YAKLAŞIK KOT : 195 m**

GÖZLEM SÜRESİ : **01.10.1997 - 30.09.2006**

ORTALAMA AKIMLAR : **Gözlem süresinde 3.668 m3/sn. (6 Yıllık) 2006 Su yılında 3.022 m3/sn.**

ANLIK EN ÇOK VE EN AZ AKIMLAR:

2006 Su yılında anlık ençok akım	**:**	**16.6**	**m3/sn**	**30.07.2006**
2006 Su yılında anlık enaz akım	**:**	**0.074**	**m3/sn**	**22.04.2006**
Gözlem süresinde anlık ençok akım	**:**	**46.6**	**m3/sn**	**01.08.2005**
Gözlem süresinde anlık enaz akım	**:**	**0.011**	**m3/sn**	**11.11.1998**

Akımlar 01 Ekim 2005 'den 30 Eylül 2006' a kadar m3/sn olarak

Gün	Ekim	Kasım	Aralık	Ocak	Şubat	Mart	Nisan	Mayıs	Haziran	Temmuz	Ağustos	Eylül
01	0.242	0.570	0.640	0.640	0.990	1.31	1.13	0.388	0.388	1.31	15.4	0.920
02	0.242	0.570	0.640	0.640	1.06	1.31	1.20	0.287	8.56	0.850	15.4	4.45
03	0.332	0.570	0.640	0.640	1.13	1.31	1.31	0.242	9.04	0.570	15.1	13.0
04	0.444	0.570	0.640	0.640	1.13	1.31	1.31	0.177	9.04	2.95	9.76	12.7
05	0.850	0.570	0.640	0.640	0.990	1.31	1.31	0.177	7.14	12.7	1.53	12.7
06	0.710	0.640	0.640	0.640	0.990	1.20	1.31	0.139	0.920	13.0	0.990	13.0
07	0.710	0.640	0.640	0.710	1.06	1.13	1.20	0.177	0.388	13.0	5.30	13.0
08	0.780	0.640	0.640	0.710	3.08	1.13	1.20	0.139	0.332	13.3	14.5	12.7
09	0.780	0.640	0.640	0.710	6.22	1.13	1.20	0.242	0.500	13.3	14.5	7.84
10	0.780	0.640	0.640	0.710	2.95	1.13	1.20	0.332	2.82	13.0	14.5	1.53
11	0.780	0.710	0.640	0.710	2.08	1.20	1.13	0.444	13.6	9.52	14.5	1.13
12	0.850	0.710	0.710	0.710	1.86	1.13	1.06	0.287	13.9	1.31	14.5	0.990
13	0.780	0.710	0.780	0.640	3.47	1.13	1.06	0.287	13.9	0.780	14.5	0.444
14	0.710	0.710	0.710	0.640	3.60	1.06	0.990	0.287	13.9	0.640	14.5	0.287
15	0.570	0.710	0.640	0.640	3.94	1.13	0.990	0.332	13.6	2.69	10.0	0.444
16	0.500	0.710	0.640	0.640	2.56	1.13	0.990	0.332	11.8	12.4	1.86	0.242
17	0.500	0.710	0.640	0.640	2.19	1.13	1.06	0.388	8.08	12.4	1.13	0.287
18	0.570	0.710	0.640	0.640	1.97	1.06	0.990	0.444	1.31	13.3	1.06	0.242
19	0.570	0.710	0.640	0.640	1.97	1.06	0.920	0.444	0.920	13.3	5.13	0.210
20	0.640	0.710	0.640	0.710	1.86	1.06	0.990	0.444	0.780	15.1	14.5	0.242
21	0.640	0.780	0.640	0.710	1.75	1.13	0.990	0.210	0.640	14.8	14.5	0.332
22	0.570	0.780	0.640	0.710	1.64	1.13	0.332	0.177	0.640	15.1	14.5	0.388
23	0.710	0.710	0.640	0.710	1.53	1.13	0.139	0.444	2.82	9.52	14.5	0.570
24	0.640	0.640	0.640	0.710	1.42	1.13	0.139	0.640	13.3	1.06	14.2	0.640
25	0.570	0.640	0.710	0.780	1.31	1.06	0.139	0.444	13.6	0.710	14.2	0.570
26	0.640	0.640	0.710	0.850	1.31	1.06	0.177	0.332	13.3	0.640	14.2	0.500
27	0.640	0.640	0.640	0.990	1.42	1.20	0.139	0.287	11.5	5.30	8.80	0.500
28	0.500	0.640	0.640	0.850	1.31	1.31	0.139	0.332	11.8	15.4	1.97	0.444
29	0.570	0.640	0.710	0.920	-----	1.20	0.177	0.242	11.5	15.4	1.31	0.388
30	0.570	0.640	0.710	0.990	-----	1.13	0.210	0.210	8.80	16.0	1.06	0.388
31	0.570	-----	0.640	0.990	-----	1.13	-----	0.210	-----	15.7	0.990	-----
Maks.	0.990	0.990	0.850	0.990	10.6	1.42	1.53	0.920	14.2	16.6	15.7	13.3
Min.	0.177	0.570	0.500	0.570	0.990	0.990	0.074	0.139	0.210	0.500	0.920	0.177
Ortalama	0.612	0.663	0.658	0.726	2.03	1.16	0.838	0.307	7.29	8.87	9.64	3.37
LT/SN/Km2	0.587	0.636	0.631	0.696	1.95	1.11	0.803	0.294	7.00	8.51	9.25	3.23
AKIM mm.	1.57	1.65	1.69	1.86	4.71	2.98	2.08	0.789	18.1	22.8	24.8	8.38
MİL. M3	1.64	1.72	1.76	1.94	4.91	3.11	2.17	0.822	18.9	23.8	25.8	8.73

SU YILI (2006) YILLIK TOPLAM AKIM 95.30 MİLYON M3 91 MM. 2.9 LT/SN/Km2

20

CEYHAN HAVZASI

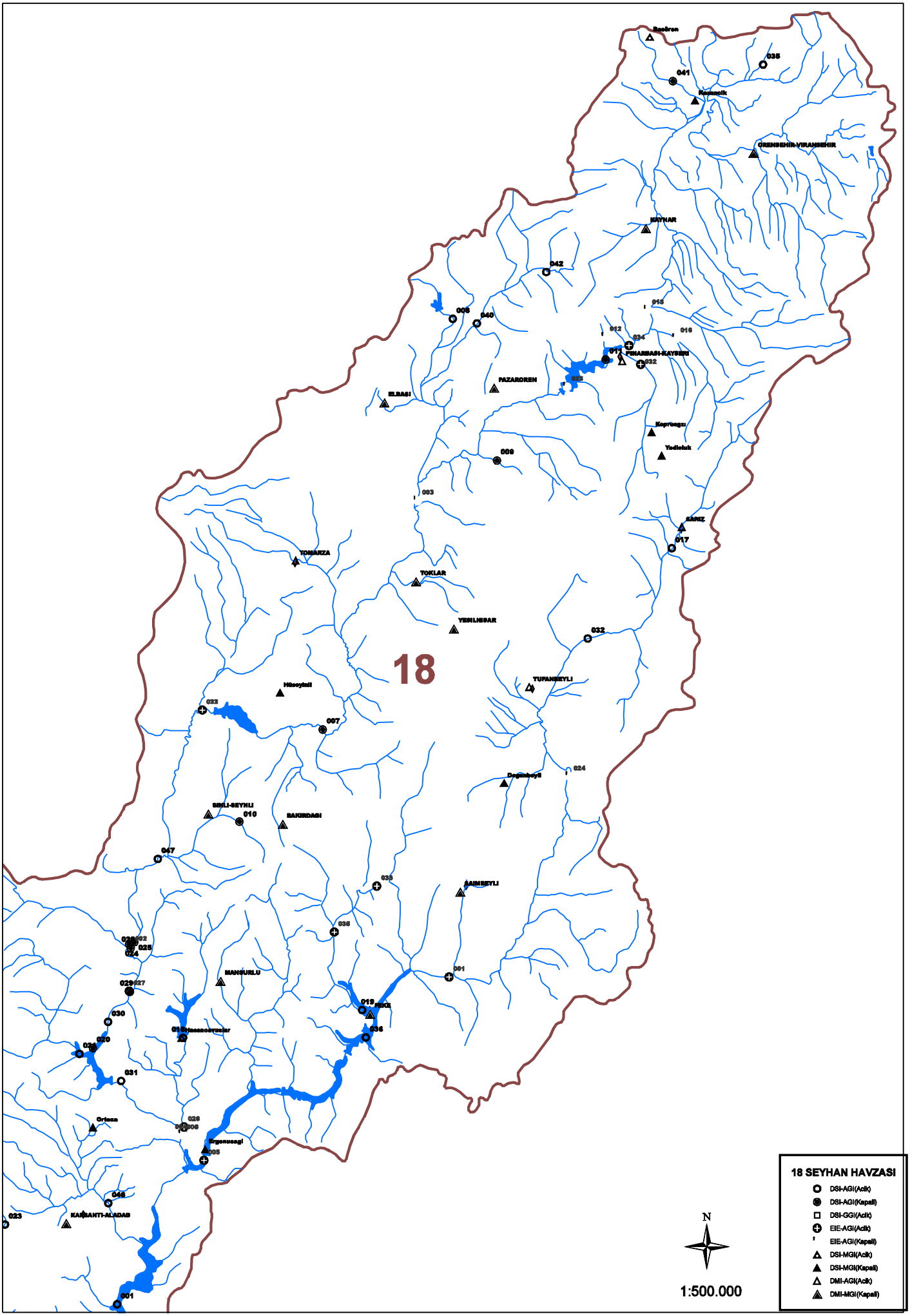
18
Basiran
041
035
Kesikcik
ORENSEHIR-YIRANSEHIR
KAYNAR
042
008
040
018
012
034
016
017
PINARBASI-KAYSERI
032
PAZAROREN
ELBASI
Kepreagzi
Yedieluk
009
003
SARIZ
017
TOMARZA
TOKLAR
YENILHISAR
032
TUFANBEYLI
Hisaydili
022
007
024
Doganhisar
SINILI-SEYHLI
010
BAKIRDAGI
047
033
SAIMBEYLI
036
025
024
MANSURLU
001
029
027
019
SIKKI
030
036
020
031
Orisca
026
Erganusagi
005
046
023
KARBANTI-ALADAG
001
N
1:500.000
18 SEYHAN HAVZASI
DSI-AGI(Acik)
DSI-AGI(Kapali)
DSI-GGI(Acik)
EIE-AGI(Acik)
EIE-AGI(Kapali)
DSI-MGI(Acik)
DSI-MGI(Kapali)
DMI-AGI(Acik)
DMI-MGI(Kapali)

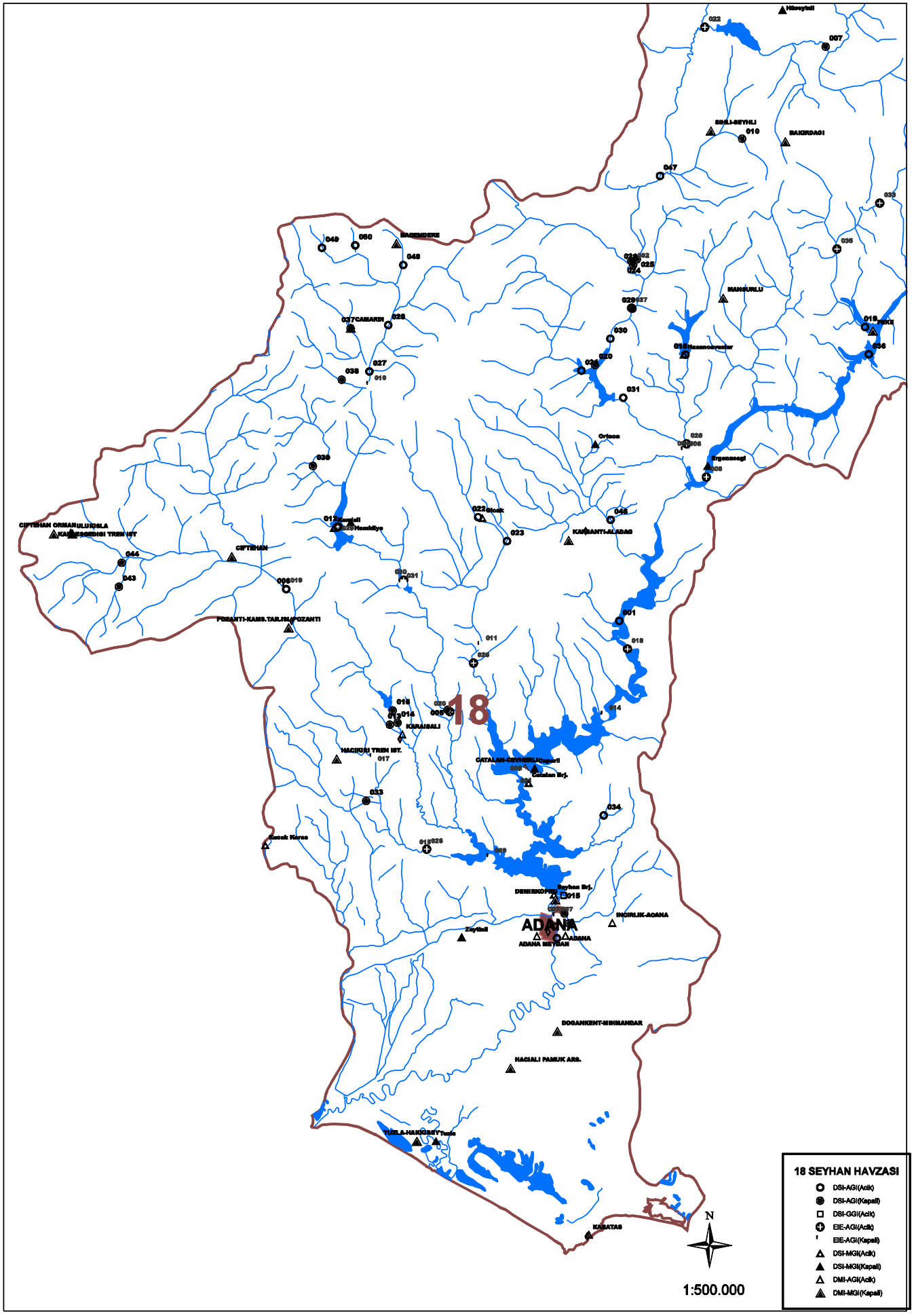
18
ADANA
SIRLI-SEYHLI
BAKIRDAGI
MAHMURLU
Hasancelyalar
Orlaca
Ergenzengi
KARBANTI-ALADAG
CAMARDI
BAKENDERE
CEYHAN ORMANLUKSILA
CEYHAN
POZANTI-KAMS.TAR.ISL.POZANTI
KARAISALI
HACIKIRI TREN IST.
CATALAN-CEVHERLIK
Catalan Brj.
Kucuk Karaa
DENIZKOPRU
Seyhan Brj.
INCIRLIK-ADANA
Zeytinli
ADANA MEYDAN
DOGANKENT-MIHMANDAR
HACIALI PAMUK ARS.
TURLA-HAKIGREY
KARATAS
N
1:500.000
18 SEYHAN HAVZASI
DSI-AGI(Acik)
DSI-AGI(Kapali)
DSI-GGI(Acik)
EIE-AGI(Acik)
EIE-AGI(Kapali)
DSI-MGI(Acik)
DSI-MGI(Kapali)
DMI-AGI(Acik)
DMI-MGI(Kapali)

20. Ceyhan Havzasi

D20A002 AKSU ÇAYİ BASPİNAR

YERİ : **GÖLBAŞI K.MARAŞ YOLUNUN 60.KM SİNDEN SAĞA AYRILAN YOLUN 16.KM.SINDEDİR. 37°27'18" Doğu - 37°41'53" Kuzey**

YAĞIŞ ALANI : **197.10 km2** **YAKLAŞIK KOT : 895 m**

GÖZLEM SÜRESİ : **22.10.1961 - 30.09.2006**

ORTALAMA AKIMLAR : **Gözlem süresinde 3.780 m3/sn. (32 Yıllık) 2006 Su yılında 2.617 m3/sn.**

ANLIK EN ÇOK VE EN AZ AKIMLAR:

2006 Su yılında anlık ençok akım	**:**	**22.0**	**m3/sn**	**08.03.2006**
2006 Su yılında anlık enaz akım	**:**	**0.532**	**m3/sn**	**01.10.2005**
Gözlem süresinde anlık ençok akım	**:**	**125.**	**m3/sn**	**24.06.1975**
Gözlem süresinde anlık enaz akım	**:**	**0.087**	**m3/sn**	**07.08.2001**

1. Anahtar Eğrisi (Seviyeler cm olarak)

Seviye	Akım	Seviye	Akım	Seviye	Akım	Seviye	Akım
30	0.062	35	0.220	40	0.748	70	10.8
31	0.087	36	0.296	45	1.6	80	15.6
32	0.111	37	0.372	50	2.9	90	22.0
33	0.147	38	0.446	55	4.5	100	31.0
34	0.184	39	0.597	60	6.7		

Akımlar 01 Ekim 2005 'den 30 Eylül 2006' a kadar m3/sn olarak

Gün	Ekim	Kasım	Aralık	Ocak	Şubat	Mart	Nisan	Mayıs	Haziran	Temmuz	Ağustos	Eylül
01	0.687	1.12	1.23	1.60	1.60	8.33	5.79	3.82	1.34	1.23	0.687	0.687
02	0.687	1.12	1.23	1.60	1.75	9.15	7.09	3.82	1.34	1.12	0.687	0.687
03	0.687	1.12	1.23	1.45	1.75	11.3	7.09	3.82	1.23	1.12	0.687	0.687
04	0.687	1.34	1.23	1.45	1.90	12.2	6.24	3.51	1.12	1.23	0.687	0.687
05	0.687	1.90	1.23	1.45	1.90	9.98	9.15	3.51	1.12	1.12	0.687	0.687
06	0.687	1.34	1.12	1.45	5.35	9.15	7.92	3.82	1.23	1.12	0.687	0.687
07	0.687	1.34	1.12	1.60	10.8	9.15	7.50	4.14	1.23	1.12	0.687	0.687
08	0.687	1.23	1.12	1.60	10.4	11.8	7.09	4.14	1.23	1.23	0.687	0.687
09	0.687	1.23	1.12	1.45	8.33	14.6	6.68	3.82	1.23	1.12	0.687	0.765
10	0.610	1.23	1.12	1.45	5.79	10.4	7.09	3.82	1.23	1.12	0.687	0.765
11	0.610	1.12	1.12	1.45	8.33	9.15	7.09	3.51	1.12	1.00	0.687	0.765
12	0.610	1.12	1.12	1.60	10.4	8.33	6.68	3.51	1.12	0.883	0.687	0.765
13	0.610	1.12	1.12	1.45	13.2	7.92	6.24	3.19	1.12	0.883	0.687	0.765
14	0.687	1.12	1.12	1.45	9.15	7.50	6.24	2.62	1.12	0.883	0.687	0.765
15	0.687	1.12	1.12	1.45	7.50	7.50	5.79	1.90	1.12	0.883	0.687	0.765
16	0.765	1.12	1.23	1.45	5.79	7.09	6.24	1.75	1.12	0.765	0.687	0.687
17	1.00	1.12	1.23	1.34	4.46	6.68	7.50	1.90	1.12	0.765	0.687	0.687
18	1.00	1.12	1.90	1.34	4.14	6.24	5.79	2.14	1.12	0.765	0.687	0.687
19	1.00	1.12	4.14	1.34	4.14	7.92	5.35	2.14	1.12	0.765	0.687	0.687
20	1.00	1.23	3.82	1.45	4.14	7.09	4.90	1.90	1.12	0.765	0.687	0.687
21	1.00	4.46	2.62	1.34	4.46	6.24	4.90	1.75	1.12	0.765	0.687	0.687
22	1.00	2.14	2.14	1.45	5.35	5.79	4.46	1.75	1.12	0.765	0.687	0.687
23	1.00	1.60	2.37	1.45	5.79	5.79	4.46	1.75	1.12	0.765	0.687	0.687
24	1.00	1.45	2.14	1.34	6.24	5.79	5.79	1.75	1.12	0.765	0.687	0.687
25	0.883	1.45	1.90	1.45	6.68	7.50	4.90	1.45	1.12	0.765	0.687	0.687
26	0.883	1.34	1.90	1.60	7.09	7.50	4.46	1.45	1.12	0.687	0.687	0.765
27	0.883	1.34	1.75	1.75	7.50	7.09	4.46	1.45	1.12	0.687	0.687	0.883
28	0.883	1.34	1.75	1.75	7.92	6.68	4.14	1.45	1.12	0.687	0.687	0.883
29	1.00	1.23	1.60	1.60	-----	6.68	4.14	1.45	1.34	0.687	0.687	0.883
30	1.12	1.23	1.60	1.60	-----	6.24	4.14	1.45	1.34	0.687	0.687	0.883
31	1.12	-----	1.60	1.60	-----	6.24	-----	1.45	-----	0.687	0.687	-----
Maks.	1.23	8.33	8.33	1.90	16.2	22.0	15.6	7.09	1.34	1.34	0.687	0.883
Min.	0.532	1.12	1.12	1.23	1.60	5.35	3.82	1.00	1.12	0.687	0.687	0.687
Ortalama	0.824	1.40	1.65	1.50	6.14	8.16	5.98	2.58	1.17	0.898	0.687	0.734
LT/SN/Km2	4.18	7.08	8.35	7.59	31.1	41.4	30.3	13.1	5.94	4.56	3.49	3.72
AKIM mm.	11.2	18.3	22.4	20.3	75.3	111.	78.6	35.0	15.4	12.2	9.34	9.65
MİL. M3	2.21	3.62	4.41	4.00	14.8	21.9	15.5	6.91	3.04	2.40	1.84	1.90

SU YILI (2006) YILLIK TOPLAM AKIM 82.53 MİLYON M3 419 MM. 13.3 LT/SN/Km2

20. Ceyhan Havzasi

D20A005 YARPUZ Ç. ÇONA

YERİ : OSMANİYE - KAHRAMANMARAŞ KARAYOLUNUN 8. KM' SİNDEN SOLA AYRILAN ÇONA KÖY YOLUNUN 3. KMSİNDEKİ ÇONA KÖYÜ YAKINLARINDADIR. 36°20'12" Doğu - 37°5'58" Kuzey

YAĞIŞ ALANI : 94,40 km2 YAKLAŞIK KOT : 265 m

GÖZLEM SÜRESİ : 07.08.1961 - 30.09.2006

ORTALAMA AKIMLAR : Gözlem süresinde 1.653 m3/sn. (42 Yıllık) 2006 Su yılında 1.462 m3/sn.

ANLIK EN ÇOK VE EN AZ AKIMLAR:

2006 Su yılında anlık ençok akım	:	27.0	m3/sn	20.01.2006
2006 Su yılında anlık enaz akım	:	0.340	m3/sn	14.12.2005
Gözlem süresinde anlık ençok akım	:	180.	m3/sn	09.02.1984
Gözlem süresinde anlık enaz akım	:	0.180	m3/sn	02.12.2001

9. Anahtar Eğrisi (Seviyeler cm olarak)

Seviye	Akım	Seviye	Akım	Seviye	Akım	Seviye	Akım
1	0.180	41	5.8	85	17.0	125	31.0
9	0.780	49	7.8	93	19.0	145	39.0
17	1.6	61	10.5	101	22.0	220	88.0
25	2.8	69	12.5	109	25.0	300	160.
33	4.2	77	14.5	117	27.0		

Akımlar 01 Ekim 2005 'den 30 Eylül 2006' a kadar m3/sn olarak

Gün	Ekim	Kasım	Aralık	Ocak	Şubat	Mart	Nisan	Mayıs	Haziran	Temmuz	Ağustos	Eylül
01	0.620	0.620	0.620	0.550	1.45	2.40	3.60	1.45	1.10	0.940	0.550	0.480
02	0.700	0.620	0.620	0.550	1.10	2.60	4.20	1.45	1.10	0.940	0.620	0.550
03	0.700	0.620	0.620	0.550	1.10	2.40	4.20	1.45	1.00	0.940	0.620	0.550
04	0.780	0.700	0.550	0.550	1.10	3.10	3.80	1.35	1.00	0.940	0.620	0.480
05	0.620	0.780	0.550	0.620	1.10	2.60	4.00	1.35	1.00	0.940	0.480	0.480
06	0.620	0.700	0.550	1.10	1.20	2.30	3.60	1.35	1.00	0.940	0.480	0.480
07	0.550	0.620	0.550	0.940	4.60	2.10	3.30	1.35	1.00	0.940	0.480	0.480
08	0.480	0.620	0.550	0.940	10.5	2.40	3.30	1.35	1.00	0.940	0.480	0.480
09	0.550	0.620	0.550	0.940	5.60	5.60	3.30	1.20	1.00	0.940	0.480	0.480
10	0.480	0.620	0.480	0.860	5.40	4.00	3.50	1.20	1.00	0.940	0.480	0.480
11	0.550	0.620	0.480	0.860	4.60	2.90	3.50	1.20	0.940	0.940	0.480	0.480
12	0.480	0.620	0.480	0.780	4.40	2.60	3.10	1.10	1.00	0.940	0.550	0.480
13	0.550	0.620	0.480	0.700	6.80	2.40	3.10	1.10	1.00	0.940	0.550	0.480
14	0.480	0.620	0.400	0.700	6.40	2.30	2.90	1.10	0.940	0.940	0.550	0.480
15	0.550	0.620	0.400	0.700	5.40	3.30	2.90	1.00	0.940	0.940	0.550	0.480
16	0.620	0.620	0.400	0.780	4.40	3.60	2.90	1.00	0.940	0.780	0.550	0.480
17	1.00	0.620	0.400	0.780	3.80	3.30	3.50	1.20	0.940	0.780	0.550	0.480
18	1.20	0.620	0.480	0.860	3.50	3.10	2.90	1.10	0.940	0.780	0.550	0.480
19	1.45	0.620	0.700	0.860	3.30	10.0	2.40	1.10	0.940	0.780	0.550	0.480
20	0.940	0.620	1.20	6.60	3.10	5.00	2.10	1.10	0.860	0.780	0.480	0.480
21	0.780	0.780	0.860	2.80	2.90	4.00	2.00	1.10	1.00	0.780	0.480	0.480
22	0.700	1.00	0.700	1.85	2.80	3.60	1.85	1.00	1.00	0.780	0.480	0.480
23	0.620	0.860	0.700	1.70	2.60	3.30	1.85	1.00	1.00	0.780	0.550	0.620
24	0.620	0.780	0.700	1.60	2.60	3.10	2.40	1.10	1.00	0.780	0.480	0.620
25	0.700	0.700	0.620	1.85	2.40	4.40	1.85	1.10	1.00	0.780	0.480	0.620
26	0.550	0.700	0.620	5.40	2.40	7.00	1.85	1.00	1.00	0.780	0.550	0.620
27	0.550	0.700	0.550	3.80	2.40	5.40	1.70	1.00	1.00	0.780	0.480	0.620
28	0.480	0.700	0.550	2.80	2.40	5.00	1.70	1.00	1.00	0.780	0.550	0.620
29	0.550	0.620	0.550	2.30	-----	4.60	1.60	1.00	1.00	0.620	0.550	0.620
30	0.620	0.620	0.480	2.00	-----	4.20	1.60	1.00	0.940	0.620	0.480	0.620
31	0.550	-----	0.480	3.80	-----	3.80	-----	1.10	-----	0.620	0.480	-----
Maks.	2.00	1.35	1.70	27.0	15.5	18.5	5.00	1.60	1.20	1.00	0.700	0.620
Min.	0.400	0.550	0.340	0.550	1.10	2.10	1.60	0.860	0.860	0.620	0.480	0.480
Ortalama	0.666	0.673	0.576	1.65	3.55	3.75	2.82	1.16	0.986	0.842	0.523	0.522
LT/SN/Km2	7.05	7.13	6.11	17.5	37.6	39.8	29.8	12.3	10.4	8.92	5.54	5.53
AKIM mm.	18.9	18.5	16.4	46.8	90.9	107.	77.3	32.9	27.1	23.9	14.8	14.3
MİL. M3	1.78	1.74	1.54	4.42	8.58	10.1	7.30	3.10	2.56	2.26	1.40	1.35

SU YILI (2006) YILLIK TOPLAM AKIM 46.13 MİLYON M3 489 MM. 15.5 LT/SN/Km2

20. Ceyhan Havzasi

D20A006 SABUN S. HARUNİYE

YERİ : **OSMANİYE İLİ DÜZİÇİ İLÇESİNE 3.5 KM UZAKLIKTA SABUN SUYU KÖPRÜSÜNÜN 500 M MENBASINDADIR 36°28'10" Doğu - 37°16'51" Kuzey**

YAĞIŞ ALANI : **174,90 km2** **YAKLAŞIK KOT : 340 m**

GÖZLEM SÜRESİ : **08.08.1961 - 30.09.2006**

ORTALAMA AKIMLAR : **Gözlem süresinde 3.763 m3/sn. (32 Yıllık) 2006 Su yılında 3.483 m3/sn.**

ANLIK EN ÇOK VE EN AZ AKIMLAR:

2006 Su yılında anlık ençok akım	**:**	**34.2**	**m3/sn**	**19.03.2006**
2006 Su yılında anlık enaz akım	**:**	**0.249**	**m3/sn**	**03.08.2006**
Gözlem süresinde anlık ençok akım	**:**	**105.**	**m3/sn**	**12.01.1967**
Gözlem süresinde anlık enaz akım	**:**	**0.002**	**m3/sn**	**23.07.1996**

14. Anahtar Eğrisi (Seviyeler cm olarak)

Seviye	Akım	Seviye	Akım	Seviye	Akım	Seviye	Akım
15	0.079	27	0.270	90	12.1	190	49.7
17	0.100	30	0.368	110	18.8	210	60.0
19	0.125	37	0.713	130	25.9	230	72.0
22	0.173	50	2.0	150	33.1	250	84.0
25	0.227	70	6.1	170	41.1	270	96.0

Akımlar 01 Ekim 2005 'den 30 Eylül 2006' a kadar m3/sn olarak

Gün	Ekim	Kasım	Aralık	Ocak	Şubat	Mart	Nisan	Mayıs	Haziran	Temmuz	Ağustos	Eylül
01	0.409	1.25	1.04	1.79	2.74	9.32	10.2	4.08	1.79	1.14	0.270	0.336
02	0.409	1.25	1.04	1.79	2.74	10.9	10.9	4.08	1.68	1.14	0.270	0.336
03	0.491	1.25	1.04	1.89	2.93	12.7	10.6	3.67	1.57	1.25	0.270	0.336
04	0.491	1.36	1.04	2.93	3.11	15.7	9.63	3.30	1.47	1.57	0.270	0.336
05	0.785	1.89	1.04	2.74	3.85	11.8	10.2	3.30	1.36	1.25	0.270	0.336
06	1.36	1.47	1.04	2.74	4.76	9.94	9.32	3.11	1.25	1.36	0.270	0.368
07	1.25	1.36	1.04	2.74	13.7	9.32	9.01	3.11	1.14	1.57	0.270	0.368
08	1.04	1.36	1.04	2.56	19.9	9.94	8.72	3.11	1.14	1.36	0.270	0.368
09	0.930	1.25	1.04	2.56	15.7	16.0	8.43	2.93	1.25	1.25	0.303	0.368
10	0.930	1.25	0.930	2.74	15.3	13.4	8.43	2.93	1.14	1.25	0.303	0.368
11	0.930	1.25	0.930	2.74	15.3	11.2	8.14	2.74	1.14	1.14	0.303	0.368
12	0.930	1.25	0.930	2.74	16.4	9.94	7.85	2.56	1.14	1.04	0.303	0.368
13	0.930	1.25	0.930	2.74	20.6	9.01	7.85	2.56	1.14	1.04	0.303	0.368
14	0.930	1.25	0.930	2.74	17.8	8.72	7.57	2.56	1.14	1.14	0.303	0.368
15	0.930	1.25	0.930	2.56	14.3	9.01	7.57	2.19	1.14	1.25	0.303	0.368
16	1.04	1.36	0.930	2.37	11.5	9.01	7.28	2.00	1.14	1.47	0.303	0.368
17	1.14	1.25	1.36	2.56	9.63	8.72	7.28	2.93	1.14	1.14	0.303	0.368
18	1.68	1.25	2.19	2.56	8.43	8.43	6.99	2.74	1.14	0.858	0.303	0.409
19	2.74	1.36	4.53	2.56	7.85	22.7	6.99	2.74	1.14	0.858	0.303	0.409
20	2.00	1.36	8.72	5.44	7.57	16.0	6.70	2.56	1.14	0.858	0.303	0.409
21	1.57	4.53	4.53	3.48	8.14	13.1	6.70	2.19	1.14	0.858	0.303	0.450
22	1.36	4.08	3.48	3.11	8.43	11.8	6.70	2.19	1.14	0.858	0.303	0.532
23	1.36	1.89	2.74	3.11	8.43	11.8	6.70	2.00	1.14	0.785	0.303	0.930
24	1.47	1.57	2.56	3.11	8.72	11.8	5.89	1.79	1.14	0.785	0.303	0.785
25	1.36	1.36	2.56	3.30	8.72	11.5	5.44	1.47	1.14	0.785	0.303	0.785
26	1.25	1.25	2.19	4.99	8.72	11.5	4.99	1.36	1.14	0.785	0.303	0.930
27	1.25	1.14	2.00	4.99	8.72	11.5	4.99	1.79	1.14	0.713	0.303	0.858
28	1.14	1.14	1.89	3.85	9.32	11.2	4.99	1.68	1.14	0.592	0.303	0.713
29	1.14	1.14	1.89	3.48	-----	11.2	4.30	1.36	1.14	0.491	0.336	0.713
30	1.47	1.14	1.79	3.30	-----	10.9	4.30	1.36	1.14	0.368	0.336	0.653
31	1.36	-----	1.79	2.93	-----	10.6	-----	1.47	-----	0.303	0.336	-----
Maks.	6.12	7.85	12.4	7.57	22.7	34.2	11.5	6.12	2.19	1.89	1.47	1.25
Min.	0.409	1.14	0.858	1.68	2.74	7.28	4.08	1.25	0.858	0.303	0.249	0.303
Ortalama	1.16	1.53	1.94	3.00	10.1	11.6	7.49	2.51	1.22	1.01	0.298	0.489
LT/SN/Km2	6.65	8.72	11.1	17.2	57.9	66.2	42.8	14.4	6.97	5.76	1.70	2.80
AKIM mm.	17.8	22.6	29.7	46.0	140.	177.	111.	38.5	18.1	15.4	4.56	7.25
MİL. M3	3.12	3.95	5.19	8.05	24.5	31.0	19.4	6.73	3.16	2.70	0.797	1.27

SU YILI (2006) YILLIK TOPLAM AKIM 109.87 MİLYON M3 628 MM. 19.9 LT/SN/Km2

20. Ceyhan Havzasi

D20A008 KARAÇAY OSMANİYE

YERİ : **OSMANİYE İLİ KARAÇAY MAHALLESİNE 2.5 KM MESAFEDEKİ BUZ FABRİKASI YAKININDADIR**
36°16'49" Doğu - 37°2'54" Kuzey

YAĞIŞ ALANI : **131,10 km2** **YAKLAŞIK KOT : 255 m**

GÖZLEM SÜRESİ : **09.08.1961 - 30.09.2006**

ORTALAMA AKIMLAR : **Gözlem süresinde 2.469 m3/sn. (41 Yıllık) 2006 Su yılında 2.338 m3/sn.**

ANLIK EN ÇOK VE EN AZ AKIMLAR:

2006 Su yılında anlık ençok akım	**:**	**22.9**	**m3/sn**	**19.03.2006**
2006 Su yılında anlık enaz akım	**:**	**0.000**	**m3/sn**	**01.10.2005**
Gözlem süresinde anlık ençok akım	**:**	**170.**	**m3/sn**	**16.05.1979**
Gözlem süresinde anlık enaz akım	**:**	**0.000**	**m3/sn**	**13.09.1990**

Akımlar 01 Ekim 2005 'den 30 Eylül 2006' a kadar m3/sn olarak

Gün	Ekim	Kasım	Aralık	Ocak	Şubat	Mart	Nisan	Mayıs	Haziran	Temmuz	Ağustos	Eylül
01	KURU	0.420	0.476	0.827	1.81	4.00	8.35	5.42	0.476	0.476	0.072	0.045
02	KURU	0.420	0.532	0.827	1.81	4.24	9.12	5.19	0.476	1.68	0.072	0.045
03	0.200	0.420	0.532	0.712	1.81	4.48	9.50	4.95	0.652	3.70	0.072	0.045
04	0.144	0.476	0.476	0.652	1.81	7.58	8.73	4.95	0.652	4.38	0.072	0.045
05	0.102	0.532	0.476	0.712	1.81	6.43	9.12	4.71	0.652	2.00	0.072	0.045
06	0.087	0.476	0.476	0.712	1.81	5.42	8.73	4.71	0.652	0.262	0.072	0.045
07	0.087	0.476	0.476	0.712	4.00	6.81	8.35	4.48	0.941	0.231	0.072	0.045
08	0.059	0.476	0.476	0.712	8.35	11.7	8.35	4.48	1.17	0.231	0.072	0.045
09	0.045	0.476	0.476	0.712	6.81	8.73	8.35	4.24	1.17	0.231	0.059	0.026
10	0.045	0.476	0.476	0.712	7.20	7.96	9.50	4.24	1.17	0.262	0.059	0.026
11	0.059	0.420	0.476	0.712	6.43	7.58	9.12	4.00	1.17	0.306	0.072	0.026
12	0.045	0.420	0.420	0.712	5.66	7.20	8.73	3.76	0.941	0.262	0.072	0.026
13	0.072	0.420	0.363	0.592	7.96	7.20	8.35	3.29	0.652	0.262	0.059	0.026
14	0.045	0.420	0.307	0.476	7.96	6.43	7.96	3.29	0.652	0.262	0.059	0.026
15	0.072	0.420	0.307	0.476	6.81	6.81	7.96	3.29	0.652	0.231	0.059	0.026
16	0.102	0.420	0.363	0.476	6.04	7.96	8.35	3.29	0.532	0.231	0.059	0.026
17	0.402	0.420	0.592	0.476	5.19	8.35	14.0	2.03	0.532	0.231	0.059	0.026
18	0.587	0.420	1.06	0.476	4.71	9.12	8.73	2.88	0.532	0.231	0.072	0.026
19	2.88	0.420	1.68	0.532	4.48	19.3	7.20	2.20	0.476	0.200	0.072	0.026
20	1.34	0.476	3.86	4.24	4.48	11.7	6.43	1.85	0.476	0.172	0.072	0.026
21	0.592	0.827	1.85	2.30	4.24	9.12	6.43	1.51	0.420	0.172	0.072	0.026
22	0.532	1.06	1.17	1.97	4.24	8.35	5.66	1.34	0.476	0.172	0.072	0.026
23	0.476	0.652	1.17	1.97	4.24	7.96	5.66	1.17	0.476	0.172	0.123	0.038
24	0.363	0.592	1.68	1.97	4.00	7.96	9.50	1.06	0.476	0.144	0.072	0.045
25	0.363	0.532	1.34	1.97	4.00	13.4	6.43	0.827	0.420	0.144	0.059	0.200
26	0.420	0.532	1.34	2.96	4.00	14.5	5.19	0.712	0.420	0.172	0.059	0.172
27	0.233	0.532	0.941	2.47	4.00	11.7	4.95	0.652	0.363	0.102	0.072	0.144
28	0.142	0.476	0.827	2.14	4.00	10.1	5.42	0.652	0.363	0.072	0.072	0.087
29	0.363	0.420	0.827	1.97	-----	9.12	5.42	0.532	0.420	0.072	0.072	0.231
30	0.532	0.420	0.827	1.81	-----	8.73	5.42	0.532	0.476	0.072	0.059	0.262
31	0.420	-----	0.827	1.81	-----	8.73	-----	0.827	-----	0.072	0.045	-----
Maks.	5.09	1.06	4.84	7.58	10.6	22.9	17.2	5.42	1.17	4.38	0.231	0.262
Min.	KURU	0.363	0.307	0.476	1.81	4.00	4.71	0.363	0.363	0.059	0.045	0.020
Ortalama	0.349	0.498	0.874	1.28	4.63	8.67	7.83	2.81	0.631	0.555	0.069	0.063
LT/SN/Km2	2.66	3.80	6.67	9.79	35.3	66.1	59.8	21.4	4.81	4.23	0.523	0.484
AKIM mm.	7.12	9.85	17.9	26.2	85.5	177.	155.	57.4	12.5	11.3	1.40	1.25
MİL. M3	0.934	1.29	2.34	3.44	11.2	23.2	20.3	7.52	1.64	1.49	0.184	0.164

SU YILI (2006) YILLIK TOPLAM AKIM 73.70 MİLYON M3 562 MM. 17.8 LT/SN/Km2

20. Ceyhan Havzasi

D20A010 HUMUS S. ARIKLIKAŞ

YERİ : **OSMANİYE İLİ BAHÇE İLÇESI TAŞOLUK KÖYÜ YAKINLARINDADIR.**
36°29'35" Doğu - 37°10'45" Kuzey

YAĞIŞ ALANI : **217,30 km2** **YAKLAŞIK KOT : 493 m**

GÖZLEM SÜRESİ : **01.10.1991 - 30.09.2006**

ORTALAMA AKIMLAR : **Gözlem süresinde 2.983 m3/sn. (14 Yıllık) 2006 Su yılında 2.657 m3/sn.**

ANLIK EN ÇOK VE EN AZ AKIMLAR:

2006 Su yılında anlık ençok akım	**:**	**49.0**	**m3/sn**	**02.02.2006**
2006 Su yılında anlık enaz akım	**:**	**0.201**	**m3/sn**	**08.05.2006**
Gözlem süresinde anlık ençok akım	**:**	**115.**	**m3/sn**	**07.03.1996**
Gözlem süresinde anlık enaz akım	**:**	**0.000**	**m3/sn**	**02.10.2002**

9. Anahtar Eğrisi (Seviyeler cm olarak)

Seviye	Akım	Seviye	Akım	Seviye	Akım	Seviye	Akım
26	0.053	50	0.506	200	30.6	290	88.0
32	0.112	80	2.2	230	47.2	300	98.0
35	0.153	110	5.6	260	66.1	310	108.
40	0.240	140	11.4	270	72.6	320	118.
45	0.353	170	19.7	280	79.0	330	128.

Akımlar 01 Ekim 2005 'den 30 Eylül 2006' a kadar m3/sn olarak

Gün	Ekim	Kasım	Aralık	Ocak	Şubat	Mart	Nisan	Mayıs	Haziran	Temmuz	Ağustos	Eylül
01	0.295	0.270	0.939	2.11	2.42	9.51	7.37	1.19	0.625	0.546	0.506	0.331
02	0.295	0.270	0.993	1.90	2.96	9.51	6.68	1.13	0.625	0.546	0.506	0.331
03	0.295	0.270	0.993	1.79	3.07	9.93	5.99	1.08	0.625	0.546	0.506	0.331
04	0.295	0.270	0.939	1.69	3.64	11.9	5.37	1.08	0.625	0.546	0.473	0.331
05	0.295	0.347	0.939	1.63	4.54	9.72	4.84	1.08	0.625	0.546	0.473	0.331
06	0.246	0.347	0.939	1.63	7.81	9.72	4.57	1.02	0.625	0.546	0.473	0.353
07	0.246	0.347	0.939	1.63	29.6	9.72	4.20	1.02	0.625	0.546	0.473	0.331
08	0.246	0.347	0.885	1.63	42.5	9.72	3.99	0.903	0.625	0.506	0.473	0.331
09	0.246	0.374	0.885	1.63	28.6	12.9	3.57	0.903	0.625	0.506	0.473	0.331
10	0.246	0.374	0.832	1.63	21.4	12.2	3.25	0.863	0.625	0.506	0.440	0.331
11	0.246	0.374	0.832	1.63	18.5	10.1	3.05	0.863	0.625	0.506	0.440	0.331
12	0.246	0.374	0.778	1.57	16.7	9.93	2.95	0.863	0.625	0.506	0.440	0.309
13	0.246	0.401	0.724	1.51	22.4	9.30	2.85	0.863	0.625	0.506	0.440	0.309
14	0.246	0.401	0.670	1.51	20.0	8.91	2.55	0.824	0.585	0.506	0.411	0.309
15	0.246	0.401	0.724	1.51	15.9	8.14	2.35	0.824	0.585	0.506	0.411	0.264
16	0.295	0.530	0.724	1.51	11.9	7.76	2.25	0.784	0.585	0.506	0.381	0.264
17	0.246	0.530	0.885	1.51	10.1	7.37	2.17	0.784	0.585	0.473	0.381	0.287
18	0.246	0.530	1.05	1.51	9.72	7.37	2.02	0.784	0.585	0.440	0.381	0.287
19	0.221	0.530	1.57	1.51	9.72	15.6	1.94	0.784	0.585	0.440	0.381	0.240
20	0.462	0.530	1.16	2.96	9.72	13.4	1.87	0.784	0.585	0.440	0.353	0.240
21	0.319	2.21	0.993	2.31	9.51	9.93	1.79	0.784	0.585	0.473	0.353	0.264
22	0.319	3.30	0.993	1.69	9.51	8.14	1.71	0.744	0.546	0.473	0.353	0.264
23	0.319	2.42	1.16	1.69	9.51	7.76	1.63	0.744	0.546	0.506	0.353	0.264
24	0.270	1.90	1.16	1.51	9.51	7.76	1.56	0.705	0.546	0.506	0.353	0.264
25	0.270	1.63	1.05	1.69	9.51	7.56	1.56	0.705	0.546	0.506	0.331	0.264
26	0.270	1.45	0.993	5.37	9.51	9.51	1.42	0.665	0.546	0.506	0.331	0.264
27	0.270	1.28	0.939	6.27	9.51	9.72	1.31	0.665	0.546	0.506	0.331	0.221
28	0.270	1.28	0.939	4.37	9.51	9.11	1.31	0.665	0.546	0.506	0.331	0.221
29	0.270	1.16	0.885	3.64	-----	9.72	1.31	0.665	0.546	0.506	0.331	0.221
30	0.270	1.10	1.28	3.07	-----	9.11	1.25	0.625	0.546	0.506	0.331	0.221
31	0.270	-----	2.42	2.73	-----	8.53	-----	0.625	-----	0.506	0.331	-----
Maks.	0.496	3.30	2.63	7.58	49.0	25.5	10.4	1.31	0.705	1.13	0.546	0.353
Min.	0.221	0.246	0.563	1.51	2.31	6.16	1.19	0.201	0.473	0.381	0.309	0.201
Ortalama	0.275	0.852	1.01	2.20	13.1	9.66	2.96	0.839	0.591	0.505	0.405	0.288
LT/SN/Km2	1.27	3.92	4.63	10.1	60.4	44.5	13.6	3.86	2.72	2.33	1.86	1.33
AKIM mm.	3.39	10.2	12.4	27.2	146.	119.	35.3	10.3	7.05	6.23	4.99	3.44
MİL. M3	0.736	2.21	2.70	5.90	31.7	25.9	7.66	2.25	1.53	1.35	1.08	0.746

SU YILI (2006) YILLIK TOPLAM AKIM 83.76 MİLYON M3 385 MM. 12.2 LT/SN/Km2

20. Ceyhan Havzasi

D20A024 CEYHAN N. HEMİTE KÖP.

YERİ : **OSMANİYE - KADİRLİ KARAYOLUNUN 24. KM' SİNDEKİ HEMİTE KÖPRÜSÜNDEDİR.**
36°5'6" Doğu - 37°11'48" Kuzey

YAĞIŞ ALANI : **15700,00 km2** **YAKLAŞIK KOT : 36 m**

GÖZLEM SÜRESİ : **18.12.1966 - 30.09.2006**

ORTALAMA AKIMLAR : **Gözlem süresinde 147.445 m3/sn. (12 Yıllık) 2006 Su yılında 108.334 m3/sn.**

ANLIK EN ÇOK VE EN AZ AKIMLAR:

2006 Su yılında anlık ençok akım	:	**329.**	**m3/sn**	**20.01.2006**
2006 Su yılında anlık enaz akım	:	**7.90**	**m3/sn**	**17.07.2006**
Gözlem süresinde anlık ençok akım	:	**2281**	**m3/sn**	**26.12.1968**
Gözlem süresinde anlık enaz akım	:	**1.00**	**m3/sn**	**01.08.1978**

Akımlar 01 Ekim 2005 'den 30 Eylül 2006' a kadar m3/sn olarak

Gün	Ekim	Kasım	Aralık	Ocak	Şubat	Mart	Nisan	Mayıs	Haziran	Temmuz	Ağustos	Eylül
01	48.7	57.9	60.2	155.	221.	210.	240.	86.5	40.3	38.3	85.0	112.
02	49.9	55.6	57.9	149.	219.	240.	240.	85.0	43.3	35.3	86.5	115.
03	61.3	48.7	53.3	139.	221.	240.	240.	82.1	51.0	40.3	86.5	73.8
04	69.7	47.6	60.2	129.	221.	226.	221.	73.8	51.0	45.3	88.0	56.7
05	66.0	45.3	54.4	124.	183.	160.	216.	89.5	44.3	52.1	88.0	56.7
06	69.7	43.3	53.3	131.	174.	185.	188.	63.7	35.3	40.3	88.0	56.7
07	71.1	40.3	82.1	114.	233.	226.	177.	56.7	30.4	48.7	86.5	57.9
08	79.3	46.4	89.5	124.	240.	190.	196.	52.1	26.3	51.0	88.0	60.2
09	73.8	49.9	126.	103.	214.	243.	141.	52.1	23.9	49.9	66.0	48.7
10	63.7	51.0	170.	73.8	151.	248.	151.	53.3	24.7	42.3	88.0	51.0
11	66.0	59.0	112.	88.0	192.	245.	174.	53.3	20.7	43.3	86.5	51.0
12	66.0	63.7	114.	103.	135.	243.	168.	78.0	22.3	99.8	92.4	54.4
13	72.4	67.1	115.	117.	137.	240.	168.	83.6	23.1	83.6	90.9	54.4
14	64.8	67.1	135.	115.	201.	240.	155.	75.2	23.1	37.3	93.9	52.1
15	60.2	101.	131.	119.	196.	226.	160.	36.3	21.5	24.7	95.3	54.4
16	54.4	112.	145.	139.	210.	221.	117.	12.0	20.7	13.3	96.8	55.6
17	78.0	155.	135.	149.	238.	194.	127.	17.4	24.7	9.28	98.3	59.0
18	114.	157.	112.	155.	238.	199.	137.	55.6	21.5	25.5	98.3	63.7
19	139.	114.	141.	164.	216.	203.	107.	54.4	34.5	30.4	98.3	76.6
20	151.	49.9	129.	177.	236.	233.	93.9	54.4	32.8	89.5	99.8	82.1
21	135.	62.5	119.	174.	236.	219.	99.8	52.1	43.3	88.0	101.	86.5
22	85.0	66.0	112.	151.	240.	212.	106.	71.1	32.0	88.0	104.	88.0
23	36.3	73.8	117.	160.	231.	224.	69.7	73.8	30.4	89.5	96.8	95.3
24	24.7	63.7	114.	166.	228.	224.	109.	109.	27.1	86.5	107.	99.8
25	27.9	47.6	112.	216.	238.	243.	104.	93.9	27.1	85.0	106.	98.3
26	46.4	42.3	112.	221.	205.	196.	96.8	80.7	29.6	86.5	106.	90.9
27	62.5	39.3	98.3	224.	238.	248.	96.8	72.4	27.9	85.0	107.	66.0
28	51.0	36.3	168.	221.	240.	245.	64.8	72.4	28.7	86.5	109.	63.7
29	40.3	62.5	179.	221.	-----	243.	104.	72.4	29.6	85.0	109.	63.7
30	41.3	63.7	172.	221.	-----	243.	89.5	67.1	40.3	83.6	109.	63.7
31	40.3	-----	164.	221.	-----	243.	-----	60.2	-----	83.6	112.	-----
Maks.	308.	321.	281.	329.	294.	305.	291.	135.	103.	107.	114.	149.
Min.	10.2	14.5	17.9	9.28	67.1	61.3	27.1	10.2	16.8	7.90	26.3	47.6
Ortalama	68.1	66.3	114.	154.	212.	224.	145.	65.8	31.0	59.6	95.7	70.3
LT/SN/Km2	4.33	4.22	7.28	9.79	13.5	14.3	9.25	4.19	1.98	3.80	6.10	4.48
AKIM mm.	11.6	10.9	19.5	26.2	32.6	38.3	24.0	11.2	5.13	10.2	16.3	11.6
MİL. M3	182.	172.	306.	412.	513.	601.	376.	176.	80.5	160.	256.	182.

SU YILI (2006) YILLIK TOPLAM AKIM 3416.50 MİLYON M3 218 MM. 6.9 LT/SN/Km2

20. Ceyhan Havzasi

D20A027 Karasu D. Inekli Gölü Çik.

YERİ : Gölbaşı Pazarcık yolunun 14.km sinden sağa ayrılan köy yolu-nun 3.km sindeki İnekli Gölü çıkışının 1.km mansabındadır.
37°29'0" Doğu - 37°47'0" Kuzey

YAĞIŞ ALANI : 211.40 km2 **YAKLAŞIK KOT :** 872 m

GÖZLEM SÜRESİ : 01.11.1970 - 30.09.2006

ORTALAMA AKIMLAR : Gözlem süresinde 2.230 m3/sn. (13 Yıllık) 2006 Su yılında 2.750 m3/sn.

ANLIK EN ÇOK VE EN AZ AKIMLAR:

2006 Su yılında anlık ençok akım	:	11.8	m3/sn	13.02.2006
2006 Su yılında anlık enaz akım	:	0.233	m3/sn	02.08.2006
Gözlem süresinde anlık ençok akım	:	11.8	m3/sn	13.02.2006
Gözlem süresinde anlık enaz akım	:	0.000	m3/sn	28.07.1986

İstasyon için kullanılmış anahtar bulunamadı.

Akımlar 01 Ekim 2005 'den 30 Eylül 2006' a kadar m3/sn olarak

Gün	Ekim	Kasım	Aralık	Ocak	Şubat	Mart	Nisan	Mayıs	Haziran	Temmuz	Ağustos	Eylül
01	3.44	2.25	2.45	2.15	2.55	9.18	4.75	3.07	1.18	0.880	0.468	0.468
02	3.50	2.25	2.40	2.15	2.70	8.83	4.75	3.01	1.14	0.762	0.360	0.522
03	3.56	2.25	2.35	2.15	2.90	8.58	4.68	2.95	1.09	0.718	0.297	0.522
04	3.56	2.30	2.35	2.15	3.07	8.49	4.54	2.90	1.09	0.762	0.360	0.576
05	3.50	2.70	2.30	2.10	3.13	8.15	4.90	2.80	1.05	0.718	0.360	0.576
06	3.50	2.55	2.25	2.10	3.62	7.81	4.68	2.80	1.05	0.718	0.414	0.576
07	3.50	2.45	2.25	2.10	5.52	7.47	4.54	2.80	0.970	0.718	0.297	0.576
08	3.44	2.40	2.20	2.05	7.98	7.56	4.39	2.75	0.970	0.674	0.360	0.468
09	3.38	2.35	2.15	2.00	8.49	7.90	4.32	2.65	0.970	0.674	0.414	0.414
10	3.32	2.30	2.15	2.00	7.47	7.47	4.17	2.60	1.00	0.576	0.414	0.468
11	3.26	2.30	2.10	2.05	9.09	7.14	4.11	2.55	1.09	0.522	0.414	0.522
12	3.26	2.25	2.10	2.10	10.4	6.89	3.99	2.45	0.970	0.522	0.414	0.522
13	3.13	2.20	2.00	2.05	11.4	6.64	3.93	2.40	1.05	0.522	0.414	0.522
14	3.01	2.20	2.00	2.05	11.1	6.48	3.87	2.30	1.00	0.522	0.468	0.576
15	2.95	2.15	1.95	2.00	10.9	6.40	3.87	2.25	1.00	0.522	0.414	0.576
16	2.85	2.15	2.00	1.95	10.7	6.24	3.87	2.15	0.970	0.522	0.414	0.576
17	2.90	2.10	2.00	1.90	10.4	6.08	4.11	2.10	0.970	0.522	0.414	0.522
18	2.90	2.10	2.00	1.90	10.4	5.91	3.99	2.05	0.940	0.522	0.414	0.630
19	2.85	2.10	2.10	1.85	10.5	6.73	3.93	2.00	0.910	0.468	0.468	0.576
20	2.80	2.15	2.20	2.00	10.5	6.32	3.93	1.90	0.880	0.468	0.468	0.576
21	2.75	3.32	2.20	2.10	10.6	6.08	3.87	1.85	0.880	0.360	0.468	0.576
22	2.60	2.80	2.10	2.10	10.6	5.91	3.80	1.80	0.880	0.468	0.414	0.674
23	2.55	2.70	2.25	2.15	10.5	5.75	3.74	1.75	0.850	0.468	0.414	0.576
24	2.50	2.65	2.25	2.20	10.4	5.67	3.74	1.70	0.806	0.414	0.414	0.674
25	2.40	2.60	2.25	2.25	10.2	5.59	3.68	1.65	0.806	0.468	0.468	0.630
26	2.35	2.60	2.35	2.40	9.99	5.52	3.56	1.45	0.806	0.522	0.414	0.630
27	2.30	2.55	2.30	2.55	9.72	5.52	3.44	1.45	0.806	0.468	0.468	0.522
28	2.25	2.55	2.25	2.60	9.45	5.36	3.38	1.36	0.850	0.468	0.468	0.718
29	2.20	2.50	2.25	2.60	-----	5.21	3.32	1.32	0.880	0.468	0.522	0.762
30	2.30	2.45	2.20	2.55	-----	4.98	3.19	1.32	0.880	0.468	0.468	0.674
31	2.30	-----	2.15	2.55	-----	4.90	-----	1.27	-----	0.414	0.414	-----
Maks.	3.68	3.80	2.50	2.65	11.8	9.36	5.21	3.19	1.27	0.940	0.630	0.850
Min.	2.20	2.05	1.95	1.80	2.55	4.83	3.13	1.23	0.718	0.297	0.233	0.414
Ortalama	2.94	2.41	2.19	2.16	8.37	6.67	4.03	2.17	0.958	0.558	0.419	0.573
LT/SN/Km2	13.9	11.4	10.4	10.2	39.6	31.6	19.1	10.3	4.53	2.64	1.98	2.71
AKIM mm.	37.2	29.5	27.7	27.3	95.8	84.5	49.5	27.5	11.7	7.07	5.30	7.03
MİL. M3	7.87	6.24	5.86	5.78	20.2	17.9	10.5	5.82	2.48	1.49	1.12	1.49

SU YILI (2006) YILLIK TOPLAM AKIM 86.75 MİLYON M3 410 MM. 13.0 LT/SN/Km2

20. Ceyhan Havzasi

D20A033 SABUN S. BOYALI

YERİ : **OSMANİYE İLİ DÜZİÇİ İLÇESİ BOYALI - BAYINDIR YOLUDAKİ SABUN SUYU KÖPRÜSÜNÜN 100 M. MANSABINDADIR.**
36°21'1" Doğu - 37°18'9" Kuzey

YAĞIŞ ALANI : **288,20 km2** **YAKLAŞIK KOT : 110 m**

GÖZLEM SÜRESİ : **01.01.1999 - 30.09.2006**

ORTALAMA AKIMLAR : **Gözlem süresinde 5.539 m3/sn. (7 Yıllık) 2006 Su yılında 6.103 m3/sn.**

ANLIK EN ÇOK VE EN AZ AKIMLAR:

2006 Su yılında anlık ençok akım	:	**52.0**	**m3/sn**	**19.03.2006**
2006 Su yılında anlık enaz akım	:	**1.39**	**m3/sn**	**24.08.2006**
Gözlem süresinde anlık ençok akım	:	**123.**	**m3/sn**	**28.10.2003**
Gözlem süresinde anlık enaz akım	:	**1.12**	**m3/sn**	**30.06.2005**

Akımlar 01 Ekim 2005 'den 30 Eylül 2006' a kadar m3/sn olarak

Gün	Ekim	Kasım	Aralık	Ocak	Şubat	Mart	Nisan	Mayıs	Haziran	Temmuz	Ağustos	Eylül
01	1.72	2.83	3.27	3.75	6.09	13.9	14.6	7.00	3.94	3.27	1.72	1.82
02	1.82	2.83	3.27	3.94	6.54	16.0	14.6	7.00	3.94	2.98	1.72	1.82
03	4.31	2.83	3.27	3.94	6.54	17.8	14.3	6.54	3.94	3.41	1.72	1.82
04	3.94	2.98	3.27	4.13	7.00	22.7	13.9	6.09	3.94	4.31	1.72	1.82
05	3.58	3.75	3.13	5.25	7.91	16.3	14.3	6.09	3.75	3.58	1.72	1.82
06	3.58	3.27	3.13	5.07	9.40	14.3	13.3	5.86	3.75	3.41	1.72	1.72
07	3.41	3.13	3.13	5.07	19.0	13.3	12.6	5.86	3.41	3.75	1.72	1.72
08	3.27	2.98	3.13	5.07	29.4	13.6	12.3	5.86	3.41	3.13	1.61	1.72
09	3.13	2.98	3.13	4.88	24.0	21.8	12.3	5.63	3.58	2.98	1.61	1.72
10	2.98	2.83	3.13	5.07	23.1	18.6	12.0	5.63	3.41	3.13	1.61	1.72
11	2.98	2.83	2.98	5.07	21.8	15.0	11.7	5.44	3.41	2.98	1.61	1.72
12	2.98	2.83	2.83	5.07	24.0	12.6	11.7	5.25	3.27	2.83	1.61	1.72
13	2.98	2.83	2.83	5.07	29.4	11.7	11.4	5.25	3.13	2.83	1.61	1.72
14	2.83	2.83	2.83	5.07	27.1	11.4	11.0	5.25	2.98	3.13	1.61	1.72
15	2.57	2.83	2.83	4.88	22.2	12.0	11.0	4.88	2.98	3.13	1.61	1.72
16	2.98	2.83	3.13	4.69	17.8	12.0	10.7	4.69	2.98	3.41	1.61	1.72
17	3.58	2.83	3.41	4.88	15.3	11.7	11.0	5.63	3.13	2.83	1.61	1.72
18	9.16	2.83	4.31	4.88	13.9	11.7	11.0	5.44	2.98	2.44	1.61	1.72
19	6.54	2.98	8.41	4.88	13.0	33.0	10.4	5.44	2.98	2.44	1.61	1.72
20	5.07	2.98	9.90	8.66	13.0	21.3	9.90	5.25	2.83	2.15	1.61	1.72
21	4.31	7.68	6.09	5.63	13.0	16.0	9.40	5.07	2.83	2.15	1.50	1.72
22	3.75	8.41	4.88	5.25	13.3	13.9	9.40	5.07	2.70	2.15	1.50	1.72
23	3.75	4.50	4.88	5.25	13.3	12.6	8.91	4.69	2.83	2.15	1.50	2.15
24	3.75	3.94	4.88	5.25	13.3	12.0	10.2	4.31	2.83	2.15	1.50	2.44
25	3.58	3.75	4.69	5.44	13.3	15.6	8.91	3.75	2.83	2.15	1.50	2.44
26	3.27	3.58	4.31	7.68	13.6	20.5	8.16	3.75	2.98	1.93	1.50	2.83
27	2.83	3.41	4.13	7.68	13.6	19.7	7.68	3.58	2.83	1.93	1.50	2.70
28	2.83	3.41	3.94	7.00	13.9	18.2	7.68	4.31	2.98	1.93	1.50	2.70
29	2.98	3.41	3.94	6.77	-----	16.7	7.68	4.13	3.13	1.93	1.50	2.70
30	3.27	3.41	3.75	6.54	-----	15.6	7.00	4.13	3.27	1.72	1.61	2.57
31	2.83	-----	3.75	6.31	-----	15.0	-----	4.13	-----	1.72	1.72	-----
Maks.	14.3	11.0	17.8	17.0	33.9	52.0	20.1	7.23	4.50	5.25	2.15	2.98
Min.	1.61	2.57	2.57	3.58	6.09	11.0	7.00	3.58	2.70	1.61	1.39	1.50
Ortalama	3.57	3.48	4.02	5.42	15.8	16.0	11.0	5.19	3.23	2.71	1.61	1.96
LT/SN/Km2	12.4	12.1	13.9	18.8	55.0	55.6	38.1	18.0	11.2	9.41	5.57	6.81
AKIM mm.	33.1	31.3	37.3	50.4	133.	149.	98.6	48.3	29.1	25.2	14.9	17.6
MİL. M3	9.55	9.03	10.8	14.5	38.3	42.9	28.4	13.9	8.38	7.26	4.30	5.09

SU YILI (2006) YILLIK TOPLAM AKIM 192.41 MİLYON M3 668 MM. 21.2 LT/SN/Km2

20. Ceyhan Havzasi

D20A040 Içerisu Ballikaya

YERİ : **NURDAĞI-GAZİANTEP YOLUNUN 5.5 KM DEN SAĞA AYRILAN HAMIDIYE YOLUNUN 4. KM SINDEDIR.**
36°52'39" Doğu - 37°8'0" Kuzey

YAĞIŞ ALANI : **79.00 km2** **YAKLAŞIK KOT : 670 m**

GÖZLEM SÜRESİ : **01.12.1972 - 30.09.2006**

ORTALAMA AKIMLAR : **Gözlem süresinde 0.530 m3/sn. (23 Yıllık) 2006 Su yılında 0.345 m3/sn.**

ANLIK EN ÇOK VE EN AZ AKIMLAR:

2006 Su yılında anlık ençok akım	**:**	**8.01**	**m3/sn**	**11.01.2006**
2006 Su yılında anlık enaz akım	**:**	**0.008**	**m3/sn**	**20.09.2006**
Gözlem süresinde anlık ençok akım	**:**	**15.0**	**m3/sn**	**21.01.1976**
Gözlem süresinde anlık enaz akım	**:**	**0.000**	**m3/sn**	**01.10.1986**

11. Anahtar Eğrisi (Seviyeler cm olarak)

Seviye	Akım	Seviye	Akım	Seviye	Akım	Seviye	Akım
8	0.001	13	0.040	30	0.850	70	13.0
9	0.003	14	0.065	35	1.5	80	17.0
10	0.005	20	0.227	40	2.2	90	21.0
11	0.015	21	0.260	50	5.0	100	25.0
12	0.026	25	0.470	60	9.0		

Akımlar 01 Ekim 2005 'den 30 Eylül 2006' a kadar m3/sn olarak

Gün	Ekim	Kasım	Aralık	Ocak	Şubat	Mart	Nisan	Mayıs	Haziran	Temmuz	Ağustos	Eylül
01	0.044	0.044	0.044	0.100	0.618	0.710	0.710	0.433	0.248	0.149	0.044	0.024
02	0.044	0.044	0.044	0.100	1.19	0.710	0.829	0.433	0.248	0.149	0.044	0.024
03	0.044	0.044	0.044	0.100	1.31	0.618	1.07	0.433	0.248	0.149	0.044	0.024
04	0.044	0.067	0.044	0.100	1.42	0.618	0.948	0.433	0.199	0.149	0.044	0.024
05	0.044	0.199	0.044	0.100	1.42	0.618	0.948	0.433	0.199	0.149	0.044	0.024
06	0.044	0.044	0.044	0.100	2.80	0.618	0.829	0.433	0.199	0.149	0.044	0.024
07	0.044	0.024	0.044	0.100	2.62	0.618	0.829	0.525	0.199	0.149	0.044	0.024
08	0.044	0.024	0.024	0.100	5.13	0.618	0.829	0.525	0.199	0.100	0.044	0.024
09	0.044	0.024	0.024	0.100	3.00	0.829	0.829	0.525	0.199	0.100	0.044	0.024
10	0.044	0.024	0.024	0.067	1.90	0.829	0.710	0.340	0.199	0.100	0.044	0.024
11	0.044	0.024	0.024	0.067	1.54	0.710	0.710	0.340	0.199	0.100	0.044	0.024
12	0.044	0.024	0.024	0.067	1.42	0.710	0.710	0.340	0.199	0.100	0.044	0.024
13	0.044	0.013	0.024	0.067	2.44	0.618	0.710	0.340	0.199	0.100	0.044	0.024
14	0.044	0.013	0.024	0.067	2.08	0.618	0.710	0.340	0.199	0.100	0.044	0.024
15	0.044	0.013	0.024	0.100	1.78	0.618	0.618	0.340	0.199	0.067	0.024	0.024
16	0.044	0.013	0.024	0.100	1.54	0.618	0.618	0.340	0.199	0.067	0.024	0.024
17	0.044	0.013	0.044	0.067	1.31	0.618	0.618	0.340	0.199	0.067	0.024	0.013
18	0.044	0.013	0.044	0.067	1.31	0.710	0.618	0.340	0.199	0.067	0.024	0.013
19	0.067	0.013	0.044	0.100	1.19	1.66	0.525	0.340	0.199	0.067	0.024	0.013
20	0.067	0.024	0.067	0.149	1.07	1.42	0.525	0.340	0.199	0.067	0.024	0.008
21	0.067	0.067	0.067	0.149	0.948	1.19	0.525	0.340	0.199	0.067	0.024	0.008
22	0.067	0.100	0.067	0.149	0.948	1.07	0.525	0.340	0.199	0.067	0.024	0.008
23	0.044	0.067	0.067	0.149	0.948	0.948	0.525	0.248	0.199	0.067	0.024	0.013
24	0.044	0.067	0.199	0.149	0.829	0.829	0.525	0.248	0.199	0.067	0.024	0.013
25	0.044	0.044	0.248	0.248	0.829	0.948	0.525	0.248	0.199	0.067	0.024	0.024
26	0.044	0.044	0.248	1.42	0.829	1.19	0.525	0.248	0.199	0.067	0.024	0.024
27	0.044	0.044	0.199	1.78	0.710	1.19	0.525	0.248	0.199	0.067	0.024	0.013
28	0.044	0.044	0.199	1.31	0.710	1.07	0.525	0.248	0.149	0.067	0.024	0.013
29	0.044	0.044	0.199	0.829	-----	1.07	0.525	0.248	0.149	0.044	0.024	0.013
30	0.044	0.044	0.149	0.618	-----	0.829	0.525	0.248	0.149	0.044	0.024	0.013
31	0.044	-----	0.149	0.525	-----	0.829	-----	0.248	-----	0.044	0.024	-----
Maks.	0.100	0.248	0.340	8.01	6.33	2.08	1.07	0.525	0.248	0.149	0.044	0.024
Min.	0.044	0.013	0.024	0.067	0.525	0.618	0.525	0.199	0.149	0.044	0.024	0.008
Ortalama	0.047	0.042	0.081	0.295	1.57	0.847	0.671	0.349	0.199	0.091	0.033	0.019
LT/SN/Km2	0.595	0.534	1.03	3.73	19.8	10.7	8.50	4.42	2.52	1.15	0.418	0.242
AKIM mm.	1.59	1.38	2.75	10.0	47.9	28.7	22.0	11.8	6.53	3.08	1.12	0.627
MİL. M3	0.126	0.109	0.217	0.790	3.79	2.27	1.74	0.935	0.516	0.243	0.088	0.050

SU YILI (2006) YILLIK TOPLAM AKIM 10.87 MİLYON M3 138 MM. 4.4 LT/SN/Km2

20. Ceyhan Havzasi

D20A043 KESİK S. TAŞKÖPRÜ

YERİ : **CEYHAN - KADİRLİ YOLUNUN 45. KM SİNDE MEHMETLİ BARAJINA GİDEN YOLUN 30 KM.SİNDE MEHMETLİ BARAJ GİRİŞİNDEKİ TAŞKÖPRÜ KÖYÜ YAKININDADIR. 36°0'13" Doğu - 37°33'31" Kuzey**

YAĞIŞ ALANI : **163,00 km2** **YAKLAŞIK KOT : 194 m**

GÖZLEM SÜRESİ : **01.09.1975 - 30.09.2006**

ORTALAMA AKIMLAR : **Gözlem süresinde 3.867 m3/sn. (31 Yıllık) 2006 Su yılında 2.787 m3/sn.**

ANLIK EN ÇOK VE EN AZ AKIMLAR:

2006 Su yılında anlık ençok akım	**:**	**18.3**	**m3/sn**	**12.02.2006**
2006 Su yılında anlık enaz akım	**:**	**0.254**	**m3/sn**	**13.09.2006**
Gözlem süresinde anlık ençok akım	**:**	**180.**	**m3/sn**	**29.12.1986**
Gözlem süresinde anlık enaz akım	**:**	**0.000**	**m3/sn**	**01.10.1992**

Akımlar 01 Ekim 2005 'den 30 Eylül 2006' a kadar m3/sn olarak

Gün	Ekim	Kasım	Aralık	Ocak	Şubat	Mart	Nisan	Mayıs	Haziran	Temmuz	Ağustos	Eylül
01	0.520	0.293	0.520	2.00	1.02	4.42	9.35	4.82	2.77	1.35	0.600	0.369
02	0.445	0.293	0.445	2.00	1.02	4.82	9.35	4.82	2.77	1.35	0.600	0.369
03	0.600	0.293	0.445	1.80	1.02	6.14	9.35	4.60	2.77	1.35	0.600	0.369
04	0.369	0.293	0.445	1.80	1.02	8.60	9.10	4.60	2.77	1.35	0.600	0.369
05	0.369	0.293	0.445	1.61	1.02	7.93	9.10	4.42	2.77	1.35	0.600	0.369
06	0.369	0.293	0.445	1.61	1.02	6.81	8.85	4.42	2.77	1.35	0.600	0.369
07	0.369	0.293	0.445	1.61	1.80	6.58	8.60	4.42	2.58	1.22	0.600	0.369
08	0.293	0.293	0.445	1.61	11.6	7.03	8.60	4.42	2.38	1.12	0.600	0.369
09	0.293	0.293	0.445	1.48	10.6	10.1	8.60	4.42	2.19	1.12	0.600	0.369
10	0.293	0.293	0.445	1.48	7.26	9.85	8.60	4.23	2.00	1.02	0.445	0.369
11	0.293	0.293	0.445	1.48	8.38	9.10	9.10	4.23	2.38	1.02	0.445	0.369
12	0.293	0.293	0.369	1.35	10.6	8.38	8.85	4.04	2.38	1.02	0.445	0.293
13	0.293	0.293	0.369	1.35	13.5	7.93	8.85	3.86	2.00	1.02	0.445	0.293
14	0.293	0.293	0.369	1.22	11.6	7.48	8.60	3.86	1.48	1.02	0.445	0.293
15	0.293	0.293	0.445	1.22	10.1	7.48	8.15	3.48	1.48	0.890	0.445	0.293
16	0.760	0.293	0.600	1.22	8.15	7.48	8.15	3.48	1.35	0.890	0.445	0.293
17	0.600	0.293	2.95	1.22	7.03	7.48	7.93	5.48	1.35	0.890	0.445	0.293
18	0.369	0.293	10.9	1.22	6.36	8.38	7.48	4.42	1.35	0.890	0.445	0.293
19	0.445	0.293	7.48	1.22	5.70	10.6	7.26	4.23	1.35	0.760	0.445	0.293
20	0.369	0.293	6.81	1.80	5.04	10.4	7.03	3.86	1.35	0.760	0.445	0.293
21	0.293	0.760	5.04	1.35	4.82	9.35	6.58	3.67	1.35	0.760	0.445	0.293
22	0.369	0.760	4.60	1.12	4.42	9.10	6.58	3.48	1.35	0.760	0.369	0.293
23	0.369	0.680	3.48	1.02	4.23	8.38	6.14	3.30	1.12	0.760	0.369	0.293
24	0.293	0.600	3.48	1.02	4.04	8.15	7.03	3.13	1.12	0.760	0.369	0.369
25	0.293	0.600	3.30	1.02	4.04	10.1	6.14	2.95	1.12	0.760	0.369	0.445
26	0.293	0.520	3.13	1.02	4.04	10.6	5.92	2.95	1.12	0.760	0.369	0.445
27	0.293	0.520	2.95	1.02	4.04	10.6	5.70	2.95	1.12	0.760	0.369	0.445
28	0.293	0.520	2.77	1.12	4.23	10.9	5.48	2.77	1.22	0.760	0.369	0.445
29	0.293	0.520	2.58	1.12	-----	9.85	5.26	2.77	1.35	0.600	0.369	0.445
30	0.293	0.520	2.58	1.12	-----	9.60	5.04	2.77	1.35	0.600	0.369	0.445
31	0.293	-----	2.19	1.02	-----	9.60	-----	2.77	-----	0.600	0.369	-----
Maks.	4.04	1.22	16.9	2.38	18.3	13.3	14.1	11.4	3.13	1.35	0.680	0.520
Min.	0.293	0.293	0.369	0.890	0.520	4.23	5.04	2.77	1.02	0.520	0.293	0.254
Ortalama	0.365	0.395	2.30	1.36	5.63	8.49	7.69	3.86	1.82	0.955	0.465	0.354
LT/SN/Km2	2.24	2.43	14.1	8.36	34.6	52.1	47.2	23.7	11.1	5.86	2.86	2.17
AKIM mm.	5.99	6.29	37.8	22.4	83.6	140.	122.	63.4	28.9	15.7	7.65	5.63
MİL. M3	0.977	1.02	6.17	3.65	13.6	22.7	19.9	10.3	4.71	2.56	1.25	0.917

SU YILI (2006) YILLIK TOPLAM AKIM 87.75 MİLYON M3 538 MM. 17.1 LT/SN/Km2

20. Ceyhan Havzasi

D20A044 DALACAK D. DAGLICAK

YERİ : **KOZAN - FEKE YOLUNUN 15. KM SİNDEKİ DALACAK MESİRE YERINDEDİR.**
35°50'10" Doğu - 37°33'18" Kuzey

YAĞIŞ ALANI : **35,00 km2** **YAKLAŞIK KOT : 425 m**

GÖZLEM SÜRESİ : **01.10.1975 - 30.09.2006**

ORTALAMA AKIMLAR : **Gözlem süresinde 0.776 m3/sn. (25 Yıllık) 2006 Su yılında 0.402 m3/sn.**

ANLIK EN ÇOK VE EN AZ AKIMLAR:

2006 Su yılında anlık ençok akım	**:**	**16.1**	**m3/sn**	**08.02.2006**
2006 Su yılında anlık enaz akım	**:**	**0.000**	**m3/sn**	**10.10.2005**
Gözlem süresinde anlık ençok akım	**:**	**105.**	**m3/sn**	**20.11.1994**
Gözlem süresinde anlık enaz akım	**:**	**0.000**	**m3/sn**	**01.10.1975**

Akımlar 01 Ekim 2005 'den 30 Eylül 2006' a kadar m3/sn olarak

Gün	Ekim	Kasım	Aralık	Ocak	Şubat	Mart	Nisan	Mayıs	Haziran	Temmuz	Ağustos	Eylül
01	0.108	0.084	0.051	0.161	0.422	0.422	0.935	0.633	0.132	0.228	0.066	0.066
02	0.108	0.084	0.051	0.161	0.422	0.422	0.935	0.633	0.132	0.270	0.066	0.066
03	0.108	0.084	0.051	0.132	0.422	0.712	0.712	0.633	0.132	0.270	0.066	0.066
04	0.108	0.228	0.051	0.132	0.367	0.824	0.712	0.555	0.108	0.270	0.066	0.066
05	0.108	0.132	0.030	0.132	0.319	0.633	0.712	0.555	0.108	0.476	0.066	0.066
06	0.108	0.108	0.030	0.132	0.270	0.555	0.712	0.555	0.108	0.367	0.066	0.066
07	KURU	0.108	0.030	0.132	0.824	0.555	0.712	0.476	0.108	0.228	0.066	0.066
08	KURU	0.108	0.051	0.132	5.24	1.05	0.712	0.476	0.108	0.161	0.066	0.066
09	KURU	0.108	0.066	0.132	2.36	2.14	0.712	0.476	0.108	0.161	0.066	0.066
10	KURU	0.108	0.066	0.132	1.56	1.42	0.633	0.476	0.108	0.161	0.066	0.066
11	KURU	0.108	0.066	0.132	3.69	1.16	0.555	0.367	0.108	0.161	0.066	0.066
12	KURU	0.108	0.066	0.132	3.91	1.05	0.712	0.319	0.108	0.108	0.066	0.066
13	KURU	0.108	0.066	0.132	6.24	0.824	0.712	0.270	0.108	0.066	0.108	0.066
14	KURU	0.108	0.066	0.132	3.91	0.824	0.712	0.319	0.108	0.066	0.132	0.066
15	KURU	0.108	0.084	0.132	3.24	1.05	0.712	0.270	0.108	0.066	0.084	0.066
16	0.041	0.108	0.108	0.132	2.14	0.935	0.712	0.270	0.108	0.066	0.084	0.066
17	0.030	0.108	0.161	0.186	1.71	0.824	0.712	0.633	0.108	0.066	0.084	0.066
18	0.030	0.108	0.712	0.186	1.27	1.16	0.712	0.422	0.108	0.066	0.084	0.066
19	0.051	0.108	3.47	0.186	1.16	1.56	0.712	0.367	0.108	0.066	0.084	0.066
20	0.108	0.108	1.27	0.712	1.05	1.27	0.712	0.319	0.108	0.066	0.084	0.066
21	0.108	0.712	0.712	0.422	0.712	1.27	0.712	0.270	0.108	0.066	0.084	0.066
22	0.084	0.319	0.555	0.367	0.712	1.16	0.555	0.270	0.108	0.066	0.084	0.066
23	0.084	0.270	0.476	0.367	0.633	1.05	0.476	0.270	0.108	0.066	0.084	0.066
24	0.084	0.270	0.367	0.367	0.555	1.05	0.824	0.228	0.108	0.066	0.084	0.066
25	0.084	0.228	0.319	0.555	0.555	1.16	0.824	0.228	0.108	0.066	0.084	0.066
26	0.084	0.084	0.270	0.935	0.476	1.16	0.712	0.228	0.108	0.066	0.084	0.066
27	0.084	0.066	0.228	0.712	0.476	1.16	0.712	0.228	0.108	0.066	0.084	0.066
28	0.084	0.051	0.228	0.712	0.476	1.05	0.633	0.270	0.108	0.066	0.084	0.066
29	0.084	0.051	0.228	0.476	-----	1.05	0.633	0.228	0.108	0.066	0.084	0.066
30	0.084	0.051	0.186	0.422	-----	0.935	0.633	0.228	0.108	0.066	0.084	0.066
31	0.084	-----	0.161	0.422	-----	0.935	-----	0.161	-----	0.066	0.084	-----
Maks.	0.476	4.13	12.4	1.56	16.1	3.91	2.80	1.85	0.422	7.58	0.228	0.108
Min.	KURU	0.051	0.021	0.132	0.132	0.422	0.476	0.132	KURU	0.030	0.051	0.051
Ortalama	0.060	0.144	0.331	0.297	1.61	1.01	0.705	0.375	0.110	0.133	0.079	0.066
LT/SN/Km2	1.71	4.13	9.47	8.48	46.0	28.9	20.2	10.7	3.15	3.79	2.27	1.89
AKIM mm.	4.58	10.7	25.4	22.7	111.	77.4	52.2	28.7	8.18	10.2	6.07	4.89
MİL. M3	0.160	0.374	0.888	0.795	3.90	2.71	1.83	1.01	0.286	0.356	0.213	0.171

SU YILI (2006) YILLIK TOPLAM AKIM 12.69 MİLYON M3 363 MM. 11.5 LT/SN/Km2

20. Ceyhan Havzasi

D20A046 KEŞİŞ S. SARIDANIŞMANLI

YERİ : **KADİRLİ - ANDIRIN YOLUNUN 25. KM SİNDEN SOLA AYRILAN KÖY YOLUNUN 5 KM SİNDEKİ SARIDANIŞMANLI KÖYÜ İÇERİSİNDEDİR.**
36°15'16" Doğu - 37°26'51" Kuzey

YAĞIŞ ALANI : **420,00 km2** **YAKLAŞIK KOT : 200 m**

GÖZLEM SÜRESİ : **01.12.1973 - 30.09.2006**

ORTALAMA AKIMLAR : **Gözlem süresinde 10.642 m3/sn. (32 Yıllık) 2006 Su yılında 8.520 m3/sn.**

ANLIK EN ÇOK VE EN AZ AKIMLAR:

2006 Su yılında anlık ençok akım	:	**87.2**	**m3/sn**	**04.03.2006**
2006 Su yılında anlık enaz akım	:	**0.273**	**m3/sn**	**17.11.2005**
Gözlem süresinde anlık ençok akım	:	**600.**	**m3/sn**	**16.05.1991**
Gözlem süresinde anlık enaz akım	:	**0.000**	**m3/sn**	**01.10.1986**

Akımlar 01 Ekim 2005 'den 30 Eylül 2006' a kadar m3/sn olarak

Gün	Ekim	Kasım	Aralık	Ocak	Şubat	Mart	Nisan	Mayıs	Haziran	Temmuz	Ağustos	Eylül
01	1.06	1.20	2.39	5.73	3.21	22.7	31.4	14.4	2.08	1.06	0.909	2.39
02	0.984	1.20	1.78	5.32	2.99	25.0	35.6	11.1	2.08	1.49	0.909	1.35
03	0.909	1.20	1.64	4.90	2.99	39.9	31.4	11.1	2.08	1.78	0.909	0.833
04	1.06	1.35	1.93	4.32	2.99	49.8	25.5	10.0	2.08	2.24	0.909	0.758
05	1.35	1.35	1.64	4.32	3.21	56.5	25.5	10.0	1.93	2.08	0.909	0.758
06	1.49	1.35	1.93	3.83	2.99	41.7	23.8	9.45	1.93	2.08	0.909	0.833
07	1.20	1.35	1.64	3.83	3.21	36.8	22.7	8.87	1.78	2.08	1.06	0.833
08	1.06	1.35	2.08	3.66	9.45	33.8	22.1	8.87	1.93	1.35	0.984	0.833
09	0.984	1.35	1.78	3.83	47.3	44.2	21.5	8.87	1.93	1.20	1.20	0.909
10	0.984	1.35	1.93	3.44	33.2	59.2	22.7	8.29	1.78	1.20	1.20	0.909
11	0.984	1.35	2.24	3.44	23.3	43.6	21.5	7.72	1.78	1.35	1.20	1.78
12	0.984	1.35	2.24	3.44	33.2	37.4	21.0	7.72	1.35	1.35	1.20	1.78
13	0.984	1.20	1.93	3.21	38.6	33.2	19.3	7.72	2.24	1.49	1.06	0.833
14	0.984	1.20	2.08	3.21	43.6	30.2	20.4	7.72	1.35	1.20	1.20	0.758
15	0.984	1.20	1.93	3.21	36.2	27.9	17.7	6.56	1.35	1.20	1.06	0.758
16	0.984	1.20	2.24	3.21	32.0	30.2	18.2	6.15	1.35	1.20	1.06	0.758
17	1.06	1.20	2.54	2.76	25.5	29.1	18.2	6.56	0.984	1.06	1.06	0.639
18	2.39	1.64	3.83	1.93	23.3	27.3	17.1	6.15	1.35	1.06	1.06	0.984
19	1.64	1.35	36.8	2.24	20.4	30.2	15.5	6.15	0.909	1.49	0.984	0.909
20	2.08	1.93	46.7	3.21	18.8	54.5	14.9	5.73	0.909	0.984	1.06	0.909
21	1.64	1.49	43.6	6.15	17.1	36.2	14.4	5.32	0.909	0.984	1.06	0.833
22	1.49	3.99	24.4	3.83	16.0	31.4	14.9	5.32	0.984	0.984	1.06	1.35
23	1.35	5.73	17.1	3.44	17.7	28.5	12.7	4.90	0.984	0.984	0.984	1.35
24	1.06	2.76	16.0	3.66	17.1	26.7	18.8	4.49	0.984	0.984	0.984	0.984
25	1.06	2.08	14.4	2.76	17.1	26.1	17.7	4.16	1.06	0.984	0.984	1.64
26	1.20	2.76	12.7	2.99	17.1	48.5	14.4	3.83	0.984	0.833	0.984	2.39
27	1.20	1.93	9.45	4.32	18.2	38.0	11.6	3.21	0.984	0.984	1.06	1.93
28	1.20	3.21	9.45	4.32	19.9	33.8	14.4	3.21	0.984	0.984	1.06	1.49
29	1.20	1.64	7.14	3.99	-----	30.8	11.6	3.21	1.20	0.984	1.20	1.49
30	1.20	1.93	7.14	3.44	-----	29.6	11.6	2.76	1.06	0.984	1.35	1.64
31	1.06	-----	5.73	3.21	-----	32.6	-----	2.24	-----	0.909	2.39	-----
Maks.	3.83	9.45	62.0	21.0	66.4	87.2	39.2	23.8	16.0	19.3	4.49	8.87
Min.	0.758	0.273	0.758	0.682	0.984	18.2	2.39	0.596	0.438	0.438	0.552	0.466
Ortalama	1.22	1.81	9.30	3.71	19.5	36.0	19.6	6.83	1.44	1.28	1.10	1.19
LT/SN/Km2	2.90	4.30	22.1	8.84	46.5	85.7	46.7	16.3	3.44	3.04	2.61	2.83
AKIM mm.	7.78	11.1	59.3	23.7	112.	229.	121.	43.6	8.91	8.13	6.99	7.33
MİL. M3	3.27	4.68	24.9	9.95	47.2	96.4	50.8	18.3	3.74	3.42	2.93	3.08

SU YILI (2006) YILLIK TOPLAM AKIM 268.67 MİLYON M3 640 MM. 20.3 LT/SN/Km2

20. Ceyhan Havzasi

D20A048 Gavur G. Sifon Çikis

YERİ : K.Maraş G.antep yolunun Kapıçam mevkiinden sola ayrılan yollun 15.km sinde Vartolar Obasındadır.
36°52'0" Doğu - 27°23'0" Kuzey

YAĞIŞ ALANI : 0.00 km2 **YAKLAŞIK KOT :** 443 m

GÖZLEM SÜRESİ : 01.06.1979 - 30.09.2006

ORTALAMA AKIMLAR : Gözlem süresinde 4.532 m3/sn. (17 Yıllık) 2006 Su yılında 3.960 m3/sn.

ANLIK EN ÇOK VE EN AZ AKIMLAR:

2006 Su yılında anlık ençok akım	:	23.2	m3/sn	13.02.2006
2006 Su yılında anlık enaz akım	:	0.000	m3/sn	08.09.2006
Gözlem süresinde anlık ençok akım	:	44.0	m3/sn	17.12.1981
Gözlem süresinde anlık enaz akım	:	0.000	m3/sn	09.07.2003

Akımlar 01 Ekim 2005 'den 30 Eylül 2006' a kadar m3/sn olarak

Gün	Ekim	Kasım	Aralık	Ocak	Şubat	Mart	Nisan	Mayıs	Haziran	Temmuz	Ağustos	Eylül
01	3.81	1.77	1.50	2.54	7.33	13.5	8.38	5.02	2.21	0.260	0.086	0.073
02	3.29	1.71	1.50	2.46	12.0	13.0	8.24	4.91	2.21	0.289	0.073	0.073
03	3.12	1.71	1.50	2.38	14.1	12.7	8.94	4.91	2.21	0.289	0.073	0.073
04	2.62	1.77	1.50	2.30	10.9	12.2	8.52	5.02	2.13	0.289	0.086	0.086
05	2.38	1.64	1.43	2.13	10.9	11.9	8.52	5.13	2.05	0.260	0.100	0.073
06	2.30	1.64	1.43	2.13	13.8	11.4	8.52	4.91	1.98	0.260	0.100	0.059
07	2.21	1.57	1.36	1.91	17.3	11.1	8.38	4.80	1.84	0.260	0.086	0.045
08	1.98	1.50	1.30	1.98	20.3	10.9	8.10	4.14	1.64	0.260	0.086	0.045
09	1.84	1.43	1.30	1.91	20.7	11.4	7.99	4.25	1.64	0.260	0.113	0.059
10	1.84	1.36	1.30	1.91	18.4	11.5	7.77	3.45	2.79	0.238	0.113	0.073
11	1.84	1.36	1.30	1.91	18.0	11.1	7.66	3.04	1.64	0.238	0.113	0.045
12	1.84	1.36	1.24	1.91	18.4	10.8	7.55	2.87	0.688	0.238	0.113	0.045
13	1.77	1.36	1.24	1.84	20.3	10.5	7.22	2.87	0.644	0.217	0.100	0.059
14	1.77	1.24	1.13	1.84	20.7	10.3	6.89	2.87	0.405	0.238	0.113	0.073
15	1.71	1.19	1.02	1.84	19.8	10.2	6.89	2.87	0.405	0.238	0.113	0.086
16	1.57	1.24	1.07	1.77	18.7	9.92	6.56	2.87	0.376	0.217	0.113	0.086
17	1.50	1.30	1.30	1.71	18.2	9.78	6.56	2.87	0.376	0.238	0.125	0.073
18	1.50	1.30	2.30	1.71	18.0	9.50	6.23	2.87	0.376	0.238	0.113	0.059
19	1.71	1.64	3.37	1.57	17.7	11.4	5.90	2.87	0.376	0.217	0.100	0.059
20	1.71	3.04	3.81	1.77	17.3	11.2	5.79	2.87	0.376	0.195	0.086	0.073
21	1.71	2.95	3.92	2.54	17.0	10.6	5.57	2.87	0.347	0.195	0.100	0.073
22	1.71	2.71	3.45	2.54	16.5	10.3	5.13	2.79	0.347	0.195	0.113	0.073
23	1.71	2.38	3.62	2.62	16.1	10.2	5.24	2.79	0.318	0.195	0.100	0.073
24	1.71	2.30	4.25	2.87	15.6	9.92	6.01	2.79	0.289	0.217	0.086	0.059
25	1.71	2.21	5.35	5.02	15.3	9.78	5.13	2.79	0.260	0.238	0.100	0.059
26	1.71	2.13	5.13	14.1	14.8	9.64	4.91	2.71	0.289	0.217	0.086	0.073
27	1.71	1.98	4.58	15.5	14.4	9.50	4.69	2.71	0.260	0.195	0.100	0.086
28	1.71	1.84	4.03	10.8	13.9	9.36	4.69	2.71	0.260	0.139	0.100	0.073
29	1.84	1.71	3.45	8.52	-----	9.08	5.24	2.62	0.260	0.086	0.086	0.073
30	1.91	1.57	2.95	8.38	-----	8.94	5.35	2.46	0.260	0.073	0.086	0.086
31	1.84	-----	2.62	7.99	-----	8.66	-----	2.30	-----	0.086	0.073	-----
Maks.	3.92	3.29	5.57	18.5	23.2	15.0	10.1	5.35	2.95	0.289	0.125	0.086
Min.	1.43	1.19	1.02	1.50	7.11	8.52	4.58	2.21	0.238	0.073	0.073	KURU
Ortalama	1.99	1.76	2.43	3.88	16.3	10.7	6.75	3.39	0.975	0.219	0.098	0.068
LT/SN/Km2	0.000	0.000	0.000	0.000	0.000	0.000	0.000	0.000	0.000	0.000	0.000	0.000
AKIM mm.	0.000	0.000	0.000	0.000	0.000	0.000	0.000	0.000	0.000	0.000	0.000	0.000
MİL. M3	5.32	4.57	6.50	10.4	39.4	28.5	17.5	9.07	2.53	0.585	0.262	0.177

SU YILI (2006) YILLIK TOPLAM AKIM 124.81 MİLYON M3 0 MM. 0.0 LT/SN/Km2

20. Ceyhan Havzasi

D20A051 Nergele Ç. Topalyusuflar

YERİ : K.MARAŞ-EKİNÖZÜ İLÇESİNİN İÇMELER YOLUNUN 5.5 KM.DE TOPAL-YUSUFLAR MEVKISINDE BULUNAN KÖPRÜDEDIR.
37°10'0" Doğu - 38°1'10" Kuzey

YAĞIŞ ALANI : 131.50 km2 **YAKLAŞIK KOT :** 1110 m

GÖZLEM SÜRESİ : 02.10.1983 - 30.09.2006

ORTALAMA AKIMLAR : Gözlem süresinde 2.374 m3/sn. (20 Yıllık) 2006 Su yılında 2.321 m3/sn.

ANLIK EN ÇOK VE EN AZ AKIMLAR:

2006 Su yılında anlık ençok akım	:	8.24	m3/sn	11.04.2006
2006 Su yılında anlık enaz akım	:	0.864	m3/sn	11.10.2005
Gözlem süresinde anlık ençok akım	:	40.0	m3/sn	07.03.1996
Gözlem süresinde anlık enaz akım	:	0.160	m3/sn	18.09.1991

Akımlar 01 Ekim 2005 'den 30 Eylül 2006' a kadar m3/sn olarak

Gün	Ekim	Kasım	Aralık	Ocak	Şubat	Mart	Nisan	Mayıs	Haziran	Temmuz	Ağustos	Eylül
01	0.992	0.922	1.13	1.35	1.13	2.07	5.38	5.16	3.59	2.17	1.51	1.13
02	0.992	0.922	1.06	1.35	1.13	2.30	6.02	5.16	3.44	2.17	1.51	1.13
03	0.992	0.922	1.13	1.35	1.13	2.42	6.02	4.95	3.44	1.97	1.35	1.13
04	0.992	1.06	1.20	1.35	1.13	2.68	5.38	4.95	3.31	1.97	1.35	1.13
05	0.922	1.13	1.13	1.35	1.13	2.81	5.16	4.80	3.31	1.97	1.35	1.13
06	0.922	1.06	1.13	1.35	1.27	2.81	5.16	4.80	3.31	1.97	1.35	1.13
07	0.922	0.992	1.06	1.35	1.87	3.06	6.44	4.80	3.31	1.97	1.35	1.13
08	0.922	0.992	1.06	1.35	2.55	4.80	6.44	4.80	3.19	1.97	1.35	1.13
09	0.922	0.992	1.06	1.27	2.30	5.59	7.54	4.80	3.19	1.87	1.35	1.13
10	0.922	0.992	1.06	1.27	1.87	4.65	7.78	4.65	3.19	1.87	1.35	1.13
11	0.922	0.922	1.06	1.27	1.97	4.04	8.01	4.65	3.06	1.87	1.35	1.13
12	0.922	0.922	1.06	1.27	2.30	3.89	7.54	4.50	3.06	1.87	1.27	1.13
13	0.922	0.922	1.06	1.27	2.55	3.74	7.31	4.50	3.06	1.77	1.27	1.13
14	0.922	0.922	1.06	1.27	2.30	3.89	7.31	4.50	3.06	1.87	1.27	1.06
15	0.922	0.922	1.06	1.27	2.07	4.04	7.31	4.35	3.06	1.77	1.27	1.06
16	0.922	0.922	1.06	1.27	1.87	3.89	7.31	4.35	2.68	1.77	1.27	1.06
17	0.922	0.922	1.06	1.27	1.77	3.74	7.08	4.35	2.42	1.77	1.27	1.06
18	0.922	0.922	1.13	1.27	1.67	3.74	6.87	4.20	2.42	1.77	1.27	1.06
19	0.992	0.922	1.97	1.27	1.59	3.74	6.44	4.20	2.42	1.67	1.27	1.06
20	0.922	0.922	2.30	1.27	1.59	3.59	6.23	4.20	2.30	1.77	1.27	1.06
21	0.922	1.06	1.97	1.20	1.59	3.44	6.44	4.20	2.30	1.67	1.27	1.06
22	0.922	1.13	1.77	1.20	1.59	3.44	6.23	4.04	2.30	1.77	1.20	1.06
23	0.922	1.06	1.67	1.20	1.59	3.59	6.02	4.04	2.30	1.67	1.20	1.06
24	0.922	1.06	1.59	1.20	1.59	4.04	6.44	4.04	2.30	1.67	1.20	1.06
25	0.922	1.06	1.59	1.20	1.59	5.80	6.23	3.89	2.17	1.67	1.20	1.06
26	0.922	1.06	1.51	1.20	1.77	5.59	5.80	3.89	2.17	1.67	1.20	1.06
27	0.922	0.992	1.43	1.20	1.87	5.16	5.38	3.74	2.17	1.67	1.20	1.06
28	0.922	1.06	1.43	1.20	1.97	4.95	5.38	3.74	2.17	1.67	1.20	0.992
29	0.922	1.06	1.43	1.13	-----	4.80	5.16	3.74	2.17	1.67	1.20	0.992
30	0.922	1.13	1.43	1.13	-----	4.80	5.16	3.59	2.17	1.51	1.20	0.992
31	0.922	-----	1.35	1.13	-----	5.16	-----	3.59	-----	1.51	1.13	-----
Maks.	1.20	1.43	2.42	1.43	3.31	6.87	8.24	5.38	3.74	2.30	1.59	1.20
Min.	0.864	0.864	0.992	1.13	1.13	1.97	5.16	3.59	2.07	1.51	1.13	0.992
Ortalama	0.933	0.996	1.32	1.26	1.74	3.94	6.37	4.36	2.77	1.80	1.28	1.08
LT/SN/Km2	7.10	7.57	10.1	9.57	13.2	30.0	48.4	33.2	21.0	13.7	9.76	8.24
AKIM mm.	19.0	19.6	26.9	25.6	32.0	80.3	125.	88.8	54.6	36.8	26.1	21.4
MİL. M3	2.50	2.58	3.54	3.37	4.21	10.6	16.5	11.7	7.17	4.83	3.44	2.81

SU YILI (2006) YILLIK TOPLAM AKIM 73.25 MİLYON M3 557 MM. 17.7 LT/SN/Km2

20. Ceyhan Havzasi

D20A053 Firniz D. Kabaktepe

YERİ : **K.MARAŞ-GÖKSUN YOLUNUN 52.KM SİNDE YENI FIRNIZ KÖPRÜSÜNÜN 20 M. MANSABINDADIR.**
36°41'0" Doğu - 37°45'0" Kuzey

YAĞIŞ ALANI : **178.50 km2** **YAKLAŞIK KOT : 648 m**

GÖZLEM SÜRESİ : **01.11.1983 - 30.09.2006**

ORTALAMA AKIMLAR : **Gözlem süresinde 5.130 m3/sn. (18 Yıllık) 2006 Su yılında 4.320 m3/sn.**

ANLIK EN ÇOK VE EN AZ AKIMLAR:

2006 Su yılında anlık ençok akım	:	**19.0**	**m3/sn**	**09.03.2006**
2006 Su yılında anlık enaz akım	:	**1.55**	**m3/sn**	**01.10.2005**
Gözlem süresinde anlık ençok akım	:	**80.0**	**m3/sn**	**29.03.1988**
Gözlem süresinde anlık enaz akım	:	**0.000**	**m3/sn**	**01.10.1988**

Akımlar 01 Ekim 2005 'den 30 Eylül 2006' a kadar m3/sn olarak

Gün	Ekim	Kasım	Aralık	Ocak	Şubat	Mart	Nisan	Mayıs	Haziran	Temmuz	Ağustos	Eylül
01	1.55	1.83	1.68	3.23	1.97	7.28	13.8	7.69	2.81	2.14	1.83	1.68
02	1.55	1.83	1.68	3.23	2.14	8.61	15.8	7.28	2.81	2.14	1.83	1.68
03	1.55	1.83	1.68	3.02	2.47	10.4	15.4	7.28	2.81	2.14	1.83	1.68
04	1.55	2.31	1.68	3.02	2.47	11.2	13.8	7.28	2.64	2.14	1.83	1.68
05	1.55	2.14	1.68	3.02	2.47	11.2	13.8	6.87	2.64	2.14	1.83	1.68
06	1.55	1.83	1.68	3.02	3.02	10.8	13.2	6.06	2.47	2.14	1.83	1.68
07	1.55	1.83	1.68	3.02	5.65	10.8	12.6	6.06	2.47	2.14	1.83	1.68
08	1.55	1.68	1.68	2.81	9.08	16.3	12.6	6.06	2.47	2.14	1.83	1.68
09	1.55	1.68	1.55	2.64	8.61	18.5	13.8	6.06	2.47	2.14	1.83	1.68
10	1.55	1.68	1.55	2.64	6.47	13.8	15.4	5.65	2.47	2.14	1.83	1.68
11	1.55	1.68	1.55	2.64	10.4	10.8	15.0	5.30	2.47	1.97	1.83	1.68
12	1.55	1.68	1.55	2.64	11.2	10.4	14.4	4.96	2.47	1.97	1.83	1.68
13	1.55	1.68	1.55	2.64	12.6	11.2	13.8	4.61	2.47	1.97	1.83	1.68
14	1.55	1.68	1.55	2.64	10.8	16.3	13.2	4.61	2.47	1.97	1.83	1.68
15	1.55	1.68	1.55	2.64	8.61	10.0	13.2	4.61	2.31	1.97	1.83	1.68
16	1.68	1.68	1.68	2.64	7.28	10.0	13.2	4.61	2.31	1.97	1.83	1.68
17	2.47	1.68	1.83	2.47	6.06	9.54	12.6	4.27	2.31	1.97	1.83	1.68
18	1.97	1.68	4.96	2.47	5.65	9.08	12.6	3.92	2.31	1.97	1.83	1.68
19	2.14	1.68	15.0	2.47	4.96	11.2	11.6	3.92	2.31	1.97	1.68	1.68
20	1.97	2.14	15.4	2.14	4.61	10.4	10.8	3.68	2.31	1.97	1.68	1.68
21	1.83	3.44	8.61	1.97	4.61	9.54	10.8	3.68	2.31	1.97	1.68	1.68
22	1.83	2.31	5.65	1.97	4.61	9.54	10.4	3.68	2.31	1.97	1.68	1.68
23	1.83	1.83	5.65	1.97	4.96	10.0	10.0	3.44	2.31	1.97	1.68	1.68
24	1.83	1.83	5.30	1.97	4.96	11.2	9.08	3.23	2.31	1.97	1.68	1.68
25	1.83	1.68	4.61	1.97	5.30	15.8	9.08	3.23	2.31	1.97	1.68	1.68
26	1.83	1.68	3.92	2.14	5.65	13.8	9.08	3.02	2.31	1.97	1.68	1.68
27	1.83	1.68	3.68	2.31	5.65	12.6	8.61	3.02	2.31	1.97	1.68	1.68
28	1.83	1.68	3.68	2.31	6.06	12.0	8.15	3.02	2.14	1.97	1.68	1.55
29	1.83	1.68	3.44	1.97	-----	12.0	8.15	3.02	2.14	1.97	1.68	1.55
30	1.83	1.68	3.23	1.97	-----	12.6	7.69	3.02	2.14	1.97	1.68	1.68
31	1.83	-----	3.23	1.97	-----	13.2	-----	3.02	-----	1.83	1.68	-----
Maks.	2.81	4.27	18.1	3.23	12.6	19.0	16.3	7.69	2.81	2.14	1.83	1.83
Min.	1.55	1.68	1.55	1.97	1.97	6.47	7.69	3.02	2.14	1.83	1.68	1.83
Ortalama	1.73	1.85	3.68	2.50	6.01	11.6	12.1	4.71	2.41	2.02	1.77	1.67
LT/SN/Km2	9.69	10.3	20.6	14.0	33.7	65.1	67.5	26.4	13.5	11.3	9.90	9.36
AKIM mm.	25.9	26.8	55.3	37.5	81.5	174.	175.	70.7	35.0	30.3	26.5	24.3
MİL. M3	4.63	4.79	9.86	6.70	14.5	31.1	31.2	12.6	6.25	5.41	4.73	4.33

SU YILI (2006) YILLIK TOPLAM AKIM 136.10 MİLYON M3 762 MM. 24.2 LT/SN/Km2

20. Ceyhan Havzasi

D20A054 Tekir D. Alikesen

YERİ : **K.MARAŞ-GÖKSUN YOLUNUN 52.KM SİNDE SAĞDAKI ALIKESEN KÖPRÜSÜ-NÜN 100 M.MANSABINDADIR**

36°40'57" Doğu - 37°47'54" Kuzey

YAĞIŞ ALANI : **207.50 km2** **YAKLAŞIK KOT : 702 m**

GÖZLEM SÜRESİ : **01.11.1983 - 30.09.2006**

ORTALAMA AKIMLAR : **Gözlem süresinde 5.102 m3/sn. (20 Yıllık) 2006 Su yılında 4.491 m3/sn.**

ANLIK EN ÇOK VE EN AZ AKIMLAR:

2006 Su yılında anlık ençok akım	:	**23.8**	**m3/sn**	**09.03.2006**
2006 Su yılında anlık enaz akım	:	**0.522**	**m3/sn**	**08.10.2005**
Gözlem süresinde anlık ençok akım	:	**85.0**	**m3/sn**	**21.12.1987**
Gözlem süresinde anlık enaz akım	:	**0.090**	**m3/sn**	**14.10.1984**

Akımlar 01 Ekim 2005 'den 30 Eylül 2006' a kadar m3/sn olarak

Gün	Ekim	Kasım	Aralık	Ocak	Şubat	Mart	Nisan	Mayıs	Haziran	Temmuz	Ağustos	Eylül
01	1.14	1.27	2.31	3.60	2.48	9.43	15.7	6.79	3.00	1.44	1.14	1.01
02	1.14	1.44	2.31	3.60	2.66	10.4	16.8	6.22	2.48	1.27	1.14	1.01
03	1.27	1.27	2.14	3.60	2.83	11.0	17.1	6.22	1.97	1.27	1.14	0.875
04	1.27	3.00	2.31	3.40	3.00	12.3	15.4	6.22	2.14	1.27	1.14	0.875
05	1.14	2.66	2.31	3.40	3.40	11.8	14.5	5.65	1.97	1.27	1.01	0.875
06	1.01	2.14	1.97	3.20	4.22	11.8	14.0	5.36	1.79	1.27	1.14	1.14
07	1.01	1.79	1.97	3.20	8.68	13.7	14.5	5.36	1.79	1.27	1.14	1.14
08	1.01	1.62	1.97	3.20	12.3	17.7	14.5	5.36	1.79	1.27	1.14	1.14
09	1.01	1.62	1.79	3.00	10.7	22.3	15.7	5.08	1.79	1.14	1.14	1.14
10	1.01	1.62	1.62	3.00	8.68	17.1	17.4	4.65	1.79	1.14	1.14	1.14
11	1.01	1.62	1.62	3.00	14.0	14.5	17.4	4.43	1.79	1.14	1.14	1.14
12	1.01	1.62	1.62	2.83	15.4	13.2	16.8	4.22	1.79	1.14	1.14	1.01
13	1.14	1.62	1.62	2.83	16.8	11.8	15.9	4.00	1.62	1.27	1.14	1.14
14	1.01	1.44	1.44	2.66	14.8	11.8	15.7	3.80	1.62	1.14	1.14	1.01
15	1.01	1.44	1.79	2.66	11.0	11.8	15.4	3.60	1.62	1.27	1.27	1.14
16	1.79	1.44	1.97	2.48	8.68	10.7	15.4	3.40	1.62	1.14	1.14	1.14
17	2.66	1.44	1.97	2.66	9.06	10.4	15.1	3.40	1.44	1.14	1.14	1.14
18	1.62	1.44	5.08	2.48	9.43	10.1	14.3	3.40	1.44	1.14	1.14	1.01
19	1.62	1.44	17.1	2.48	7.65	11.3	13.2	3.20	1.27	1.14	1.01	1.14
20	1.44	1.62	17.1	2.66	5.36	11.3	11.8	3.20	1.44	1.01	1.14	1.14
21	1.44	4.00	9.80	2.48	4.43	10.1	11.8	3.20	1.44	1.14	1.01	1.14
22	1.44	4.00	6.79	2.48	6.22	9.43	11.0	3.20	1.44	1.14	1.14	1.27
23	1.44	3.00	6.79	2.48	7.36	10.4	10.1	3.20	1.27	1.14	1.01	1.44
24	1.27	2.66	5.93	2.31	7.94	13.2	9.06	3.20	1.27	1.01	1.14	1.44
25	1.27	2.31	5.36	2.48	8.68	18.1	9.80	3.00	1.44	1.01	1.01	1.62
26	1.27	2.14	4.65	2.48	9.06	16.8	8.68	3.00	1.27	1.27	1.14	1.44
27	1.27	2.14	4.22	2.66	9.43	15.1	7.94	3.00	1.27	1.14	1.01	1.27
28	1.14	1.97	4.22	2.48	8.68	14.5	7.36	3.00	1.44	1.14	1.01	1.97
29	1.27	2.31	4.00	2.48	-----	14.3	7.08	3.00	1.79	1.14	1.01	1.79
30	1.27	2.31	3.80	2.48	-----	14.3	7.08	3.00	1.79	1.14	1.01	1.62
31	1.27	-----	3.80	2.48	-----	15.4	-----	3.00	-----	1.14	1.01	-----
Maks.	5.65	10.7	21.5	3.80	17.4	23.8	17.7	9.43	3.00	1.97	2.48	2.83
Min.	0.522	0.566	0.566	0.875	2.66	9.43	6.79	2.48	0.566	0.566	1.01	0.522
Ortalama	1.28	2.01	4.24	2.81	8.32	13.1	13.2	4.11	1.69	1.18	1.10	1.21
LT/SN/Km2	6.17	9.70	20.4	13.6	40.1	63.1	63.7	19.8	8.13	5.68	5.31	5.84
AKIM mm.	16.5	25.1	54.7	36.3	97.0	169.	165.	53.0	21.1	15.2	14.2	15.1
MİL. M3	3.43	5.22	11.4	7.54	20.1	35.1	34.3	11.0	4.37	3.16	2.95	3.14

SU YILI (2006) YILLIK TOPLAM AKIM 141.71 MİLYON M3 683 MM. 21.6 LT/SN/Km2

20. Ceyhan Havzasi

D20A056 Bertiz Ç. Himmetli

YERİ : **K.MARAŞ-KAYSERİ YOLUNUN 7.KM SINDEN SAĞA AYRILAN YOLUN 50.KMDE BERTIZ YOLUNUN HIMMETLI MEVKIINDEDIR.**
37°2'0" Doğu - 37°14'0" Kuzey

YAĞIŞ ALANI : **238.40 km2** **YAKLAŞIK KOT : 750 m**

GÖZLEM SÜRESİ : **08.08.1984 - 30.09.2006**

ORTALAMA AKIMLAR : **Gözlem süresinde 1.938 m3/sn. (14 Yıllık) 2006 Su yılında 1.938 m3/sn.**

ANLIK EN ÇOK VE EN AZ AKIMLAR:

2006 Su yılında anlık ençok akım	**:**	**16.9**	**m3/sn**	**09.03.2006**
2006 Su yılında anlık enaz akım	**:**	**0.053**	**m3/sn**	**05.09.2006**
Gözlem süresinde anlık ençok akım	**:**	**36.0**	**m3/sn**	**04.01.1996**
Gözlem süresinde anlık enaz akım	**:**	**0.000**	**m3/sn**	**01.10.1988**

İstasyon için kullanılmış anahtar bulunamadı.

Akımlar 01 Ekim 2005 'den 30 Eylül 2006' a kadar m3/sn olarak

Gün	Ekim	Kasım	Aralık	Ocak	Şubat	Mart	Nisan	Mayıs	Haziran	Temmuz	Ağustos	Eylül
01	0.131	0.436	0.502	0.770	0.634	4.68	7.32	2.90	0.568	0.370	0.075	0.064
02	0.103	0.436	0.502	0.770	0.770	6.58	8.80	2.90	0.568	0.333	0.075	0.064
03	0.159	0.436	0.502	0.770	0.770	10.6	10.6	2.90	0.568	0.297	0.075	0.064
04	0.131	0.634	0.502	0.770	0.700	13.6	8.30	2.60	0.568	0.297	0.075	0.064
05	0.131	0.840	0.436	0.770	0.770	10.6	9.80	2.60	0.568	0.224	0.075	0.053
06	0.131	0.634	0.436	0.700	1.45	8.80	7.64	2.60	0.502	0.980	0.075	0.053
07	0.103	0.502	0.436	0.700	4.46	11.3	7.48	2.60	0.502	0.297	0.075	0.053
08	0.103	0.502	0.436	0.700	7.64	15.6	7.48	2.90	0.436	0.187	0.075	0.053
09	0.103	0.436	0.436	0.770	6.58	15.9	8.30	2.60	0.370	0.131	0.075	0.053
10	0.075	0.436	0.436	0.700	4.02	12.3	8.80	2.45	0.370	0.131	0.075	0.053
11	0.075	0.436	0.436	0.700	4.24	11.6	8.80	2.30	0.370	0.131	0.075	0.053
12	0.075	0.436	0.370	0.700	5.32	7.64	7.64	2.00	0.370	0.131	0.075	0.053
13	0.075	0.436	0.370	0.634	7.64	7.00	7.32	2.00	0.436	0.131	0.075	0.053
14	0.075	0.436	0.370	0.634	6.58	6.58	7.00	1.55	0.370	0.131	0.075	0.053
15	0.075	0.436	0.370	0.634	4.90	6.16	7.00	1.45	0.333	0.103	0.075	0.053
16	0.103	0.436	0.436	0.568	4.02	5.32	7.00	1.25	0.333	0.103	0.075	0.053
17	0.502	0.436	0.502	0.502	3.50	5.32	6.58	1.35	0.297	0.103	0.075	0.053
18	0.333	0.370	0.770	0.502	3.20	5.32	4.90	1.25	0.260	0.103	0.075	0.053
19	0.700	0.370	5.74	0.502	3.05	7.00	4.68	1.15	0.297	0.103	0.064	0.053
20	0.568	0.502	4.90	0.502	2.75	7.00	4.46	1.15	0.297	0.103	0.064	0.053
21	0.436	2.75	2.90	0.568	2.60	6.16	4.46	1.05	0.260	0.103	0.064	0.053
22	0.436	1.70	1.85	0.568	2.60	5.74	4.24	0.980	0.260	0.075	0.064	0.053
23	0.436	0.910	1.55	0.568	2.75	5.74	3.80	0.980	0.224	0.075	0.064	0.053
24	0.436	0.770	1.35	0.568	3.20	7.64	4.46	0.910	0.224	0.075	0.064	0.064
25	0.370	0.634	1.25	0.568	3.35	13.9	4.02	0.770	0.224	0.075	0.064	0.064
26	0.370	0.634	1.15	0.634	3.65	10.6	3.65	0.770	0.224	0.075	0.064	0.064
27	0.370	0.634	0.980	0.700	3.65	8.80	3.35	1.05	0.224	0.075	0.064	0.064
28	0.370	0.502	0.980	0.700	4.46	7.80	3.05	1.05	0.260	0.075	0.064	0.064
29	0.370	0.502	0.910	0.700	-----	7.32	3.05	0.840	0.502	0.075	0.064	0.064
30	0.634	0.502	0.910	0.634	-----	7.16	3.05	0.634	0.436	0.075	0.064	0.064
31	0.502	-----	0.840	0.634	-----	7.64	-----	0.634	-----	0.075	0.064	-----
Maks.	1.05	3.80	8.80	0.770	8.80	16.9	11.0	2.90	0.568	3.50	0.075	0.064
Min.	0.075	0.370	0.370	0.502	0.634	4.46	3.05	0.568	0.224	0.075	0.064	0.053
Ortalama	0.274	0.637	1.08	0.650	3.54	8.63	6.23	1.68	0.374	0.169	0.070	0.057
LT/SN/Km2	1.15	2.67	4.54	2.73	14.9	36.2	26.2	7.06	1.57	0.709	0.295	0.239
AKIM mm.	3.07	6.93	12.2	7.30	36.0	96.9	67.8	18.9	4.07	1.90	0.791	0.620
MİL. M3	0.733	1.65	2.90	1.74	8.58	23.1	16.2	4.51	0.969	0.453	0.189	0.148

SU YILI (2006) YILLIK TOPLAM AKIM 61.17 MİLYON M3 257 MM. 8.1 LT/SN/Km2

20. Ceyhan Havzasi

D20A057 Çemrengeç S. Koscagiz

YERİ : K.Maraş-Kayseri yolunun 32.km sinde Süleymanlıdan sonrabatıya doğru 7 km lik mesafedeki Koscağız Köyündedir.
36°47'0" Doğu - 37°52'0" Kuzey

YAĞIŞ ALANI : 224.30 km2 **YAKLAŞIK KOT :** 925 m

GÖZLEM SÜRESİ : 16.08.1984 - 30.09.2006

ORTALAMA AKIMLAR : Gözlem süresinde 2.384 m3/sn. (12 Yıllık) 2006 Su yılında 2.143 m3/sn.

ANLIK EN ÇOK VE EN AZ AKIMLAR:

2006 Su yılında anlık ençok akım	:	14.2	m3/sn	08.03.2006
2006 Su yılında anlık enaz akım	:	0.103	m3/sn	11.08.2006
Gözlem süresinde anlık ençok akım	:	28.8	m3/sn	25.03.2002
Gözlem süresinde anlık enaz akım	:	0.070	m3/sn	29.08.2005

Akımlar 01 Ekim 2005 'den 30 Eylül 2006' a kadar m3/sn olarak

Gün	Ekim	Kasım	Aralık	Ocak	Şubat	Mart	Nisan	Mayıs	Haziran	Temmuz	Ağustos	Eylül
01	0.290	0.500	0.800	1.54	0.980	6.20	7.51	3.64	1.21	1.10	0.135	0.135
02	0.360	0.680	0.800	1.43	1.10	6.36	8.02	3.48	1.10	1.04	0.135	0.135
03	0.360	0.740	0.800	1.43	1.10	7.00	7.68	3.48	1.04	1.04	0.135	0.135
04	0.360	1.87	0.740	1.32	1.21	7.68	7.00	3.32	1.04	0.980	0.119	0.135
05	0.360	1.98	0.740	1.32	1.32	7.17	6.84	3.16	0.980	0.920	0.119	0.135
06	0.360	1.21	0.740	1.32	1.87	7.34	6.52	3.00	0.920	0.860	0.119	0.119
07	0.360	1.04	0.740	1.32	4.76	8.02	6.36	3.00	0.860	0.800	0.119	0.119
08	0.290	0.920	0.680	1.32	4.92	11.1	6.52	3.00	0.860	0.740	0.119	0.119
09	0.290	0.920	0.680	1.21	4.28	11.1	6.68	3.48	0.860	0.740	0.119	0.135
10	0.290	0.860	0.680	1.21	3.48	9.55	6.84	3.00	0.860	0.680	0.119	0.119
11	0.290	0.860	0.620	1.10	5.56	8.53	6.68	2.68	0.800	0.680	0.103	0.135
12	0.220	0.800	0.620	1.10	6.36	7.85	6.20	2.36	0.800	0.620	0.119	0.135
13	0.220	0.800	0.620	1.04	7.00	7.51	6.04	2.20	0.740	0.560	0.119	0.135
14	0.220	0.740	0.620	1.04	5.88	7.51	5.88	2.20	0.740	0.560	0.103	0.135
15	0.220	0.740	0.680	0.980	5.08	7.34	5.88	1.98	0.740	0.500	0.103	0.135
16	0.500	0.740	0.860	0.920	4.28	7.00	5.88	1.87	0.680	0.430	0.103	0.135
17	1.43	0.740	0.860	0.920	3.64	6.84	5.72	1.87	0.680	0.360	0.119	0.135
18	0.740	0.740	5.08	0.920	3.48	6.68	5.40	1.87	0.680	0.360	0.119	0.135
19	0.860	0.800	9.55	0.920	3.16	6.84	5.08	1.76	0.680	0.290	0.119	0.135
20	0.800	0.920	7.85	0.980	3.32	6.36	4.92	1.65	0.680	0.290	0.119	0.135
21	0.620	3.48	5.08	0.920	3.64	6.20	4.76	1.54	0.680	0.220	0.103	0.150
22	0.560	2.36	3.80	0.920	4.12	6.36	4.60	1.54	0.680	0.220	0.103	0.150
23	0.500	1.65	3.32	0.920	4.44	6.84	4.44	1.54	0.680	0.220	0.103	0.220
24	0.500	1.10	2.84	0.920	4.76	7.85	4.92	1.43	0.680	0.150	0.103	0.290
25	0.500	0.980	2.52	0.920	5.08	9.38	4.76	1.43	0.740	0.150	0.103	0.290
26	0.430	0.920	2.20	0.920	5.40	8.36	4.28	1.43	0.740	0.135	0.103	0.290
27	0.430	0.860	1.98	0.980	5.56	8.02	4.12	1.32	0.740	0.135	0.103	0.290
28	0.430	0.860	1.87	0.980	5.72	7.68	3.96	1.32	1.43	0.135	0.119	0.290
29	0.430	0.800	1.76	0.920	-----	7.51	3.96	1.32	1.32	0.135	0.119	0.290
30	0.500	0.800	1.76	0.980	-----	7.51	3.80	1.32	1.21	0.135	0.119	0.290
31	0.500	-----	1.65	0.980	-----	7.51	-----	1.32	-----	0.135	0.135	-----
Maks.	4.12	6.68	12.9	1.65	7.68	14.2	8.19	3.64	7.85	1.21	0.150	0.430
Min.	0.150	0.430	0.620	0.800	0.980	5.72	3.64	1.32	0.680	0.135	0.103	0.119
Ortalama	0.459	1.08	2.05	1.09	3.98	7.65	5.71	2.21	0.862	0.494	0.115	0.173
LT/SN/Km2	2.05	4.82	9.14	4.85	17.8	34.1	25.4	9.85	3.84	2.20	0.514	0.771
AKIM mm.	5.48	12.5	24.5	13.0	42.9	91.4	66.0	26.4	9.96	5.90	1.38	2.00
MİL. M3	1.23	2.80	5.49	2.91	9.63	20.5	14.8	5.92	2.23	1.32	0.309	0.448

SU YILI (2006) YILLIK TOPLAM AKIM 67.59 MİLYON M3 301 MM. 9.6 LT/SN/Km2

20. Ceyhan Havzasi

D20A058 Tahta S. Canbazköy

YERİ : **ANDIRIN CAMBAZKÖY YOLUNUN 22.KM SİNDEDIR.**
36°17'0" Doğu - 37°40'0" Kuzey

YAĞIŞ ALANI : **24.38 km2** **YAKLAŞIK KOT : 1000 m**

GÖZLEM SÜRESİ : **06.10.1984 - 30.09.2006**

ORTALAMA AKIMLAR : **Gözlem süresinde 1.083 m3/sn. (21 Yıllık) 2006 Su yılında 1.083 m3/sn.**

ANLIK EN ÇOK VE EN AZ AKIMLAR:

2006 Su yılında anlık ençok akım	**:**	**8.30**	**m3/sn**	**19.12.2005**
2006 Su yılında anlık enaz akım	**:**	**0.378**	**m3/sn**	**01.10.2005**
Gözlem süresinde anlık ençok akım	**:**	**42.8**	**m3/sn**	**04.08.2002**
Gözlem süresinde anlık enaz akım	**:**	**0.095**	**m3/sn**	**29.09.1991**

Akımlar 01 Ekim 2005 'den 30 Eylül 2006' a kadar m3/sn olarak

Gün	Ekim	Kasım	Aralık	Ocak	Şubat	Mart	Nisan	Mayıs	Haziran	Temmuz	Ağustos	Eylül
01	0.378	0.378	0.378	0.584	0.457	2.35	3.06	1.32	0.626	0.584	0.431	0.405
02	0.378	0.378	0.378	0.584	0.499	3.06	3.06	1.32	0.626	0.584	0.457	0.405
03	0.378	0.378	0.378	0.584	0.499	5.20	3.06	1.32	0.626	0.584	0.457	0.405
04	0.378	0.378	0.378	0.584	0.499	5.20	2.87	1.19	0.626	0.584	0.431	0.405
05	0.378	0.378	0.378	0.499	0.499	4.03	2.48	1.19	0.626	0.584	0.431	0.405
06	0.378	0.378	0.378	0.499	0.626	3.26	2.48	1.19	0.626	0.584	0.431	0.405
07	0.378	0.378	0.378	0.499	2.22	3.26	2.48	1.19	0.626	0.584	0.431	0.405
08	0.378	0.378	0.378	0.499	4.03	4.42	2.48	1.19	0.626	0.584	0.431	0.405
09	0.378	0.378	0.378	0.499	3.26	5.60	2.67	1.19	0.626	0.584	0.431	0.405
10	0.378	0.378	0.378	0.499	2.48	4.23	3.06	1.09	0.626	0.584	0.431	0.405
11	0.378	0.378	0.378	0.499	4.42	3.45	2.87	0.981	0.626	0.584	0.431	0.405
12	0.378	0.378	0.378	0.499	4.81	3.06	2.48	0.981	0.626	0.584	0.431	0.378
13	0.378	0.378	0.378	0.457	4.62	2.67	2.48	0.981	0.626	0.584	0.405	0.378
14	0.378	0.378	0.378	0.457	4.03	2.48	2.35	0.981	0.626	0.584	0.405	0.378
15	0.378	0.378	0.378	0.457	3.26	2.87	2.35	0.981	0.626	0.584	0.405	0.378
16	0.378	0.378	0.378	0.457	2.48	2.48	2.35	0.981	0.626	0.584	0.405	0.378
17	0.378	0.378	0.541	0.457	2.09	2.67	2.35	0.877	0.626	0.584	0.405	0.378
18	0.378	0.378	4.23	0.457	1.96	2.87	2.09	0.877	0.584	0.584	0.405	0.378
19	0.378	0.378	5.01	0.457	1.70	4.42	1.96	0.877	0.584	0.541	0.431	0.378
20	0.378	0.378	4.42	0.457	1.70	3.45	1.96	0.877	0.584	0.457	0.405	0.405
21	0.378	0.378	2.22	0.457	1.70	3.06	1.83	0.877	0.584	0.457	0.405	0.405
22	0.378	0.772	1.57	0.457	1.70	2.67	1.70	0.877	0.584	0.457	0.405	0.405
23	0.378	0.457	1.45	0.457	1.70	2.48	1.70	0.877	0.584	0.457	0.405	0.405
24	0.378	0.431	1.32	0.457	1.70	2.48	1.83	0.877	0.584	0.457	0.405	0.405
25	0.378	0.405	1.09	0.457	1.70	4.81	1.70	0.877	0.584	0.457	0.405	0.405
26	0.378	0.405	0.877	0.499	1.96	4.03	1.57	0.877	0.584	0.457	0.405	0.405
27	0.378	0.405	0.877	0.499	2.09	3.45	1.45	0.772	0.584	0.457	0.405	0.405
28	0.378	0.405	0.626	0.499	2.35	3.26	1.32	0.668	0.584	0.457	0.405	0.405
29	0.378	0.405	0.626	0.457	-----	3.26	1.32	0.626	0.584	0.457	0.405	0.405
30	0.378	0.378	0.584	0.457	-----	3.06	1.45	0.626	0.584	0.457	0.405	0.378
31	0.378	-----	0.584	0.457	-----	3.06	-----	0.626	-----	0.457	0.405	-----
Maks.	0.378	1.96	8.30	0.584	6.20	8.00	3.26	1.70	0.626	0.584	0.457	0.405
Min.	0.378	0.378	0.378	0.457	0.457	2.09	1.32	0.626	0.584	0.405	0.378	0.378
Ortalama	0.378	0.400	1.03	0.488	2.18	3.44	2.23	0.973	0.608	0.533	0.418	0.397
LT/SN/Km2	15.5	16.4	42.4	20.0	89.4	141.	91.3	39.9	24.9	21.9	17.1	16.3
AKIM mm.	41.5	42.5	114.	53.6	216.	378.	237.	107.	64.6	58.6	45.9	42.2
MİL. M3	1.01	1.04	2.77	1.31	5.27	9.21	5.77	2.61	1.58	1.43	1.12	1.03

SU YILI (2006) YILLIK TOPLAM AKIM 34.15 MİLYON M3 1401 MM. 44.4 LT/SN/Km2

20. Ceyhan Havzasi

D20A059 Kesis D. Kelesli

YERİ : **ANDIRIN-KELEŞLİ OBASI YOLUNUN 4.KM SINDEDIR.**
36°18'44" Doğu - 37°35'10" Kuzey

YAĞIŞ ALANI : **171.50 km2** **YAKLAŞIK KOT : 1025 m**

GÖZLEM SÜRESİ : **07.10.1984 - 30.09.2006**

ORTALAMA AKIMLAR : **Gözlem süresinde 3.173 m3/sn. (22 Yıllık) 2006 Su yılında 2.679 m3/sn.**

ANLIK EN ÇOK VE EN AZ AKIMLAR:

2006 Su yılında anlık ençok akım	**:**	**33.8**	**m3/sn**	**03.03.2006**
2006 Su yılında anlık enaz akım	**:**	**0.062**	**m3/sn**	**06.09.2006**
Gözlem süresinde anlık ençok akım	**:**	**191.**	**m3/sn**	**27.11.1989**
Gözlem süresinde anlık enaz akım	**:**	**0.040**	**m3/sn**	**12.09.1995**

Akımlar 01 Ekim 2005 'den 30 Eylül 2006' a kadar m3/sn olarak

Gün	Ekim	Kasım	Aralık	Ocak	Şubat	Mart	Nisan	Mayıs	Haziran	Temmuz	Ağustos	Eylül
01	0.154	0.220	0.258	1.03	0.524	9.84	11.6	3.32	0.770	0.372	0.132	0.098
02	0.154	0.258	0.258	0.940	0.562	13.9	12.0	3.09	0.685	0.334	0.110	0.098
03	0.220	0.258	0.258	0.940	0.562	22.2	11.2	2.86	0.600	0.334	0.110	0.086
04	0.258	0.258	0.220	0.855	0.562	23.4	10.5	2.40	0.562	0.334	0.110	0.086
05	0.198	0.296	0.220	0.855	0.600	17.3	10.5	2.31	0.562	0.372	0.110	0.074
06	0.176	0.258	0.220	0.855	0.770	15.0	9.50	2.31	0.562	0.410	0.086	0.074
07	0.176	0.258	0.220	0.770	2.40	13.9	9.16	2.21	0.562	0.600	0.098	0.074
08	0.154	0.220	0.220	0.770	5.32	21.1	8.82	2.21	0.600	0.486	0.110	0.074
09	0.154	0.220	0.220	0.685	4.24	25.0	8.82	2.21	0.600	0.448	0.110	0.074
10	0.154	0.220	0.220	0.685	3.32	18.0	9.16	2.12	0.562	0.448	0.110	0.074
11	0.154	0.220	0.198	0.685	7.18	15.4	8.48	2.02	0.600	0.410	0.110	0.074
12	0.154	0.220	0.198	0.600	11.2	13.5	8.14	1.93	0.562	0.410	0.098	0.062
13	0.154	0.198	0.198	0.600	10.9	12.0	7.49	1.93	0.562	0.334	0.110	0.062
14	0.154	0.198	0.198	0.600	8.48	11.2	7.18	1.83	0.562	0.372	0.110	0.062
15	0.154	0.198	0.198	0.562	6.56	13.1	6.87	1.74	0.524	0.372	0.110	0.062
16	0.220	0.198	0.524	0.562	5.32	12.0	6.56	1.74	0.524	0.334	0.110	0.062
17	0.486	0.198	0.685	0.524	4.47	10.9	6.25	1.64	0.486	0.296	0.098	0.062
18	0.296	0.220	8.82	0.524	4.01	12.0	5.94	1.64	0.448	0.258	0.086	0.062
19	0.410	0.258	13.1	0.524	3.78	17.7	5.32	1.55	0.448	0.220	0.086	0.062
20	0.296	0.296	11.2	0.562	3.78	12.7	4.70	1.55	0.410	0.220	0.098	0.074
21	0.258	1.45	3.78	0.524	4.01	11.2	4.47	1.45	0.448	0.220	0.098	0.074
22	0.220	0.940	2.21	0.562	4.47	10.5	4.24	1.45	0.448	0.198	0.098	0.086
23	0.220	0.486	2.31	0.562	4.70	10.5	4.01	1.37	0.410	0.198	0.086	0.086
24	0.220	0.410	2.02	0.562	5.32	10.5	5.32	1.28	0.410	0.176	0.086	0.086
25	0.198	0.372	1.74	0.562	5.94	22.6	4.24	1.20	0.372	0.176	0.074	0.086
26	0.198	0.334	1.45	0.600	6.56	17.7	3.55	1.11	0.334	0.154	0.086	0.098
27	0.198	0.334	1.28	0.600	8.14	15.8	3.32	1.11	0.372	0.154	0.074	0.098
28	0.198	0.296	1.20	0.562	9.16	14.2	3.09	1.03	0.372	0.154	0.086	0.086
29	0.198	0.296	1.11	0.562	-----	12.7	3.09	0.940	0.372	0.110	0.086	0.086
30	0.220	0.258	1.11	0.562	-----	12.3	3.09	0.855	0.334	0.110	0.098	0.086
31	0.220	-----	1.03	0.524	-----	12.0	-----	0.770	-----	0.110	0.086	-----
Maks.	1.11	3.09	21.1	1.11	13.1	33.8	12.0	4.70	0.855	1.11	0.132	0.098
Min.	0.132	0.198	0.198	0.486	0.524	8.14	2.63	0.770	0.296	0.086	0.074	0.062
Ortalama	0.214	0.328	1.83	0.655	4.74	14.8	6.89	1.78	0.502	0.294	0.099	0.078
LT/SN/Km2	1.25	1.91	10.7	3.82	27.7	86.5	40.2	10.4	2.93	1.72	0.576	0.452
AKIM mm.	3.34	4.96	28.7	10.2	66.9	232.	104.	27.8	7.59	4.60	1.54	1.17
MİL. M3	0.572	0.851	4.91	1.75	11.5	39.8	17.9	4.77	1.30	0.788	0.264	0.201

SU YILI (2006) YILLIK TOPLAM AKIM 84.61 MİLYON M3 493 MM. 15.6 LT/SN/Km2

20. Ceyhan Havzasi

D20A062 Deliçay Jandarmalar Oba

YERİ : **K.Maraş-Adana karayolunun 7.km sinden sağa ayrılan yolun 14.km sinde Jandarmalar Obasında köprünün ayağındadır.**
36°48'13" Doğu - 37°28'33" Kuzey

YAĞIŞ ALANI : **132.00 km2** **YAKLAŞIK KOT : 545 m**

GÖZLEM SÜRESİ : **13.01.1987 - 30.09.2006**

ORTALAMA AKIMLAR : **Gözlem süresinde 1.272 m3/sn. (1 Yıllık) 2006 Su yılında 1.272 m3/sn.**

ANLIK EN ÇOK VE EN AZ AKIMLAR:

2006 Su yılında anlık ençok akım	**:**	**8.30 m3/sn**	**08.02.2006**
2006 Su yılında anlık enaz akım	**:**	**0.080 m3/sn**	**20.07.2006**
Gözlem süresinde anlık ençok akım	**:**	**8.30 m3/sn**	**08.02.2006**
Gözlem süresinde anlık enaz akım	**:**	**0.080 m3/sn**	**20.07.2006**

Akımlar 01 Ekim 2005 'den 30 Eylül 2006' a kadar m3/sn olarak

Gün	Ekim	Kasım	Aralık	Ocak	Şubat	Mart	Nisan	Mayıs	Haziran	Temmuz	Ağustos	Eylül
01	0.250	0.595	1.03	1.90	3.10	2.68	2.82	0.855	0.250	0.405	0.140	0.140
02	0.250	0.595	1.03	1.70	3.94	2.82	2.82	0.595	0.250	0.290	0.140	0.140
03	0.290	0.710	1.03	1.28	3.94	2.82	3.52	0.595	0.250	0.160	0.140	0.105
04	0.290	1.03	1.03	1.28	3.80	2.68	3.52	0.595	0.250	0.160	0.140	0.080
05	0.290	1.03	1.03	1.28	3.94	2.68	3.38	0.595	0.250	0.210	0.140	0.105
06	0.250	1.03	1.03	1.05	5.48	3.10	3.38	0.595	0.250	0.230	0.140	0.105
07	0.250	1.03	1.03	1.05	7.02	3.10	3.38	0.710	0.250	0.230	0.160	0.105
08	0.250	1.03	0.710	1.05	7.86	3.24	3.38	0.710	0.250	0.230	0.185	0.105
09	0.250	1.00	0.595	1.05	6.46	4.36	3.38	0.710	0.250	0.230	0.185	0.105
10	0.250	1.00	0.595	1.05	6.04	4.36	3.38	0.710	0.250	0.185	0.160	0.105
11	0.250	1.00	0.595	1.05	6.04	4.08	2.68	0.710	0.405	0.160	0.160	0.105
12	0.250	1.00	0.595	1.05	6.04	3.80	2.54	0.710	0.480	0.140	0.160	0.105
13	0.250	1.00	0.595	1.05	5.90	3.52	2.54	0.710	0.330	0.140	0.160	0.105
14	0.250	1.00	0.595	1.03	5.34	3.38	2.28	0.710	0.405	0.140	0.160	0.105
15	0.250	1.00	0.595	1.00	5.20	3.24	2.28	0.595	1.00	0.140	0.160	0.105
16	0.290	1.03	1.00	1.00	4.50	3.24	2.28	0.595	1.00	0.140	0.160	0.105
17	0.330	1.03	1.00	1.00	3.94	3.10	2.03	0.595	0.595	0.140	0.160	0.105
18	0.405	1.03	1.05	1.00	3.38	2.96	1.70	0.595	0.595	0.140	0.160	0.105
19	0.405	1.03	2.54	1.00	3.38	3.10	1.05	0.595	0.250	0.140	0.160	0.105
20	0.405	1.50	3.80	1.00	3.38	3.66	1.05	0.595	0.250	0.080	0.160	0.105
21	0.405	1.90	2.82	0.855	3.38	3.38	0.855	0.290	0.595	0.080	0.160	0.105
22	0.405	1.90	2.28	0.855	3.38	3.38	0.855	0.290	0.595	0.080	0.140	0.105
23	0.405	1.00	2.15	1.00	3.24	3.38	1.03	0.290	0.710	0.080	0.140	0.105
24	0.405	0.595	2.15	1.05	3.10	3.38	1.05	0.290	0.595	0.080	0.140	0.105
25	0.330	0.595	2.15	2.03	2.82	3.38	1.05	0.250	0.595	0.080	0.140	0.140
26	0.330	0.480	2.15	3.24	2.68	3.38	1.28	0.250	0.595	0.080	0.140	0.185
27	0.330	0.480	2.15	3.10	2.68	3.38	1.00	0.250	0.480	0.080	0.140	0.250
28	0.330	0.595	2.15	3.10	2.68	3.38	1.00	0.250	0.480	0.080	0.140	0.250
29	0.855	1.00	2.15	3.10	-----	3.38	1.00	0.250	0.480	0.080	0.140	0.250
30	0.855	1.03	2.03	3.10	-----	3.10	1.00	0.330	0.405	0.080	0.140	0.250
31	0.710	-----	1.90	2.96	-----	2.82	-----	0.330	-----	0.080	0.140	-----
Maks.	0.855	2.28	4.22	3.66	8.30	4.50	3.52	1.00	1.00	0.405	0.185	0.250
Min.	0.230	0.480	0.595	0.855	2.68	2.68	0.855	0.250	0.250	0.080	0.140	0.080
Ortalama	0.357	0.975	1.47	1.52	4.38	3.30	2.12	0.521	0.445	0.147	0.151	0.130
LT/SN/Km2	2.70	7.39	11.1	11.5	33.2	25.0	16.0	3.95	3.37	1.12	1.15	0.982
AKIM mm.	7.24	19.1	29.8	30.9	80.3	66.9	41.6	10.6	8.73	2.99	3.07	2.55
MİL. M3	0.956	2.53	3.94	4.08	10.6	8.84	5.49	1.40	1.15	0.395	0.405	0.336

SU YILI (2006) YILLIK TOPLAM AKIM 40.12 MİLYON M3 304 MM. 9.6 LT/SN/Km2

20. Ceyhan Havzasi

D20A063 Orcan Ç. Jandarmalar

YERİ : **K.Maraş-Adana karayolunun 7.km sinde eski köprü üzerindensağa ayrıldıktan sonra 15.km mesafedeki Jandarmalar Obasındadır. 36°48'0" Doğu - 37°28'30" Kuzey**

YAĞIŞ ALANI : **57.50 km2** **YAKLAŞIK KOT : 550 m**

GÖZLEM SÜRESİ : **09.01.1987 - 30.09.2006**

ORTALAMA AKIMLAR : **Gözlem süresinde 0.379 m3/sn. (1 Yıllık) 2006 Su yılında 0.379 m3/sn.**

ANLIK EN ÇOK VE EN AZ AKIMLAR:

2006 Su yılında anlık ençok akım	**:**	**3.93 m3/sn**	**07.02.2006**
2006 Su yılında anlık enaz akım	**:**	**0.049 m3/sn**	**30.06.2006**
Gözlem süresinde anlık ençok akım	**:**	**3.93 m3/sn**	**07.02.2006**
Gözlem süresinde anlık enaz akım	**:**	**0.049 m3/sn**	**30.06.2006**

Akımlar 01 Ekim 2005 'den 30 Eylül 2006' a kadar m3/sn olarak

Gün	Ekim	Kasım	Aralık	Ocak	Şubat	Mart	Nisan	Mayıs	Haziran	Temmuz	Ağustos	Eylül
01	0.207	0.280	0.360	0.450	0.765	0.450	0.400	0.145	0.318	0.049	0.092	0.092
02	0.207	0.280	0.360	0.400	1.37	0.450	0.400	0.117	0.318	0.064	0.092	0.092
03	0.240	0.280	0.360	0.400	1.54	0.450	0.540	0.117	0.318	0.078	0.092	0.078
04	0.240	0.360	0.318	0.400	1.37	0.450	0.540	0.117	0.280	0.078	0.092	0.064
05	0.240	0.318	0.280	0.400	1.45	0.450	0.540	0.117	0.207	0.092	0.092	0.064
06	0.207	0.490	0.280	0.360	2.55	0.400	0.490	0.117	0.175	0.092	0.092	0.078
07	0.207	0.490	0.280	0.318	3.79	0.400	0.450	0.145	0.175	0.117	0.117	0.078
08	0.207	0.490	0.280	0.318	3.52	0.450	0.450	0.145	0.175	0.145	0.145	0.078
09	0.207	0.360	0.280	0.318	3.25	0.885	0.450	0.145	0.175	0.117	0.145	0.078
10	0.175	0.360	0.280	0.318	2.65	0.825	0.400	0.145	0.175	0.078	0.117	0.078
11	0.207	0.280	0.280	0.318	2.65	0.765	0.360	0.145	0.207	0.078	0.117	0.078
12	0.175	0.175	0.280	0.318	2.65	0.645	0.360	0.092	0.207	0.078	0.117	0.078
13	0.175	0.145	0.280	0.318	3.13	0.540	0.360	0.092	0.175	0.064	0.117	0.078
14	0.175	0.145	0.280	0.318	2.65	0.540	0.360	0.092	0.207	0.064	0.117	0.078
15	0.175	0.207	0.280	0.318	2.15	0.540	0.360	0.092	0.207	0.064	0.117	0.078
16	0.207	0.280	0.318	0.318	1.79	0.490	0.360	0.092	0.207	0.064	0.117	0.078
17	0.240	0.280	0.400	0.318	1.29	0.490	0.318	0.092	0.145	0.064	0.117	0.078
18	0.280	0.280	0.490	0.318	1.08	0.595	0.280	0.092	0.078	0.064	0.117	0.078
19	0.280	0.280	0.645	0.318	0.945	0.945	0.240	0.092	0.078	0.064	0.117	0.078
20	0.280	0.450	1.37	0.318	0.945	0.705	0.240	0.092	0.078	0.064	0.117	0.078
21	0.280	0.885	0.765	0.318	0.885	0.645	0.240	0.078	0.078	0.064	0.117	0.078
22	0.280	0.825	0.595	0.318	0.825	0.645	0.240	0.078	0.078	0.064	0.092	0.078
23	0.280	0.490	0.595	0.360	0.765	0.645	0.240	0.078	0.078	0.064	0.092	0.078
24	0.280	0.450	0.765	0.400	0.645	0.645	0.240	0.078	0.078	0.064	0.092	0.078
25	0.280	0.400	0.705	0.645	0.595	0.645	0.240	0.078	0.078	0.064	0.092	0.092
26	0.280	0.400	0.705	1.45	0.540	0.645	0.240	0.078	0.078	0.064	0.092	0.145
27	0.280	0.318	0.645	1.01	0.490	0.540	0.207	0.078	0.078	0.064	0.092	0.207
28	0.280	0.318	0.490	1.01	0.450	0.540	0.207	0.078	0.064	0.064	0.092	0.207
29	0.318	0.360	0.490	0.705	-----	0.540	0.207	0.092	0.064	0.064	0.092	0.207
30	0.318	0.360	0.490	0.595	-----	0.490	0.145	0.145	0.049	0.064	0.092	0.207
31	0.280	-----	0.490	0.645	-----	0.400	-----	0.240	-----	0.064	0.092	-----
Maks.	0.360	0.945	1.62	1.62	3.93	1.01	0.540	0.240	0.318	0.145	0.145	0.207
Min.	0.175	0.145	0.280	0.318	0.450	0.400	0.145	0.064	0.049	0.049	0.078	0.064
Ortalama	0.242	0.368	0.466	0.462	1.67	0.576	0.337	0.109	0.154	0.074	0.106	0.098
LT/SN/Km2	4.20	6.40	8.10	8.03	29.0	10.0	5.86	1.90	2.68	1.28	1.84	1.70
AKIM mm.	11.3	16.6	21.7	21.5	70.2	26.8	15.2	5.08	6.95	3.43	4.93	4.41
MİL. M3	0.647	0.954	1.25	1.24	4.04	1.54	0.873	0.292	0.400	0.197	0.284	0.254

SU YILI (2006) YILLIK TOPLAM AKIM 11.97 MİLYON M3 208 MM. 6.6 LT/SN/Km2

20. Ceyhan Havzasi

D20A065 Çepele D. Imamoglu

YERİ : **ADANA İLİ İMAMOĞLU İLÇESİ SU DEPOSU YANINDADIR.**
35°39'14" Doğu - 37°15'57" Kuzey

YAĞIŞ ALANI : **100,00 km2** **YAKLAŞIK KOT : 100 m**

GÖZLEM SÜRESİ : **01.10.1989 - 30.09.2006**

ORTALAMA AKIMLAR : **Gözlem süresinde 0.898 m3/sn. (17 Yıllık) 2006 Su yılında 0.211 m3/sn.**

ANLIK EN ÇOK VE EN AZ AKIMLAR:

2006 Su yılında anlık ençok akım	:	**10.0**	**m3/sn**	**12.02.2006**
2006 Su yılında anlık enaz akım	:	**0.000**	**m3/sn**	**01.10.2005**
Gözlem süresinde anlık ençok akım	:	**86.0**	**m3/sn**	**20.11.1994**
Gözlem süresinde anlık enaz akım	:	**0.000**	**m3/sn**	**30.06.1990**

2. Anahtar Eğrisi (Seviyeler cm olarak)

Seviye	Akım	Seviye	Akım	Seviye	Akım	Seviye	Akım
1	0.004	26	0.328	200	20.0	370	38.0
5	0.023	40	1.1	240	25.0	380	39.0
9	0.049	80	5.0	280	29.0	515	52.5
13	0.084	120	10.3	320	33.0	850	86.0
20	0.186	160	15.7	360	37.0		

Akımlar 01 Ekim 2005 'den 30 Eylül 2006' a kadar m3/sn olarak

Gün	Ekim	Kasım	Aralık	Ocak	Şubat	Mart	Nisan	Mayıs	Haziran	Temmuz	Ağustos	Eylül
01	KURU	KURU	KURU	0.018	0.013	0.668	0.500	0.095	KURU	KURU	KURU	KURU
02	KURU	KURU	KURU	0.018	0.013	0.556	0.500	0.095	KURU	KURU	KURU	KURU
03	KURU	KURU	KURU	0.018	0.013	0.612	0.456	0.095	KURU	KURU	KURU	KURU
04	KURU	KURU	KURU	0.018	0.013	0.556	0.412	0.095	KURU	KURU	KURU	KURU
05	KURU	KURU	KURU	0.013	0.013	0.500	0.370	0.095	KURU	KURU	KURU	KURU
06	KURU	KURU	KURU	0.013	0.013	0.500	0.412	0.095	KURU	KURU	KURU	KURU
07	KURU	KURU	KURU	0.013	0.035	0.500	0.328	0.120	KURU	KURU	KURU	KURU
08	KURU	KURU	KURU	0.013	4.78	0.500	0.328	0.106	KURU	KURU	KURU	KURU
09	KURU	KURU	KURU	0.013	2.50	0.780	0.298	0.095	KURU	KURU	KURU	KURU
10	KURU	KURU	KURU	0.013	1.58	0.780	0.267	0.095	KURU	KURU	KURU	KURU
11	KURU	KURU	KURU	0.013	1.74	0.780	0.267	0.095	KURU	KURU	KURU	KURU
12	KURU	KURU	KURU	0.013	3.10	0.844	0.245	0.084	KURU	KURU	KURU	KURU
13	KURU	KURU	KURU	0.013	5.96	0.844	0.245	0.065	KURU	KURU	KURU	KURU
14	KURU	KURU	KURU	0.013	4.23	0.724	0.225	0.042	KURU	KURU	KURU	KURU
15	KURU	KURU	KURU	0.013	3.60	0.780	0.206	0.029	KURU	KURU	KURU	KURU
16	KURU	KURU	0.018	0.013	2.70	0.844	0.245	0.029	KURU	KURU	KURU	KURU
17	KURU	KURU	0.018	0.013	2.10	0.724	0.206	0.029	KURU	KURU	KURU	KURU
18	0.018	KURU	0.075	0.013	1.74	0.724	0.206	0.023	KURU	KURU	KURU	KURU
19	KURU	KURU	1.10	0.013	1.50	1.26	0.186	0.023	KURU	KURU	KURU	KURU
20	KURU	KURU	0.168	0.023	1.34	0.908	0.186	0.023	KURU	KURU	KURU	KURU
21	KURU	KURU	0.065	0.023	1.10	0.908	0.186	0.023	KURU	KURU	KURU	KURU
22	KURU	KURU	0.035	0.018	1.04	0.724	0.186	0.023	KURU	KURU	KURU	KURU
23	KURU	KURU	0.029	0.018	0.908	0.724	0.186	0.018	KURU	KURU	KURU	KURU
24	KURU	KURU	0.023	0.018	0.844	0.724	0.225	0.013	KURU	KURU	KURU	KURU
25	KURU	KURU	0.018	0.023	0.844	0.844	0.298	0.013	KURU	KURU	KURU	KURU
26	KURU	KURU	0.018	0.023	0.724	0.724	0.206	0.008	KURU	KURU	KURU	KURU
27	KURU	KURU	0.018	0.018	0.724	0.612	0.135	0.004	KURU	KURU	KURU	KURU
28	KURU	KURU	0.018	0.018	0.668	0.612	0.120	0.004	KURU	KURU	KURU	KURU
29	KURU	KURU	0.018	0.018	-----	0.500	0.106	KURU	KURU	KURU	KURU	KURU
30	KURU	KURU	0.018	0.013	-----	0.500	0.095	KURU	KURU	KURU	KURU	KURU
31	KURU	-----	0.018	0.013	-----	0.500	-----	KURU	-----	KURU	KURU	-----
Maks.	0.042	KURU	2.90	0.049	10.0	2.50	0.500	0.120	KURU	KURU	KURU	KURU
Min.	KURU	KURU	KURU	0.008	0.013	0.456	0.095	KURU	KURU	KURU	KURU	KURU
Ortalama	0.001	KURU	0.053	0.016	1.57	0.702	0.261	0.049	KURU	KURU	KURU	KURU
LT/SN/Km2	0.006	0.000	0.535	0.159	15.7	7.02	2.61	0.495	0.000	0.000	0.000	0.000
AKIM mm.	0.016	0.000	1.43	0.426	37.9	18.8	6.77	1.33	0.000	0.000	0.000	0.000
MİL. M3	0.002	0.000	0.143	0.043	3.79	1.88	0.677	0.133	0.000	0.000	0.000	0.000

SU YILI (2006) YILLIK TOPLAM AKIM 6.67 MİLYON M3 67 MM. 2.1 LT/SN/Km2

20. Ceyhan Havzasi

D20A068 KÖPRÜAĞZI D. GEBEN

YERİ : **ANDIRIN-GEBEN KASABASI İÇERİSİNDEDİR.**
36°26'17" Doğu - 37°47'18" Kuzey

YAĞIŞ ALANI : **55.00 km2** **YAKLAŞIK KOT : 1275 m**

GÖZLEM SÜRESİ : **15.05.1992 - 30.09.2006**

ORTALAMA AKIMLAR : **Gözlem süresinde 1.221 m3/sn. (6 Yıllık) 2006 Su yılında 1.371 m3/sn.**

ANLIK EN ÇOK VE EN AZ AKIMLAR:

2006 Su yılında anlık ençok akım	:	**9.94**	**m3/sn**	**08.03.2006**
2006 Su yılında anlık enaz akım	:	**0.000**	**m3/sn**	**01.10.2005**
Gözlem süresinde anlık ençok akım	:	**31.6**	**m3/sn**	**03.03.2005**
Gözlem süresinde anlık enaz akım	:	**0.000**	**m3/sn**	**01.10.1993**

Akımlar 01 Ekim 2005 'den 30 Eylül 2006' a kadar m3/sn olarak

Gün	Ekim	Kasım	Aralık	Ocak	Şubat	Mart	Nisan	Mayıs	Haziran	Temmuz	Ağustos	Eylül
01	KURU	0.154	0.474	1.20	0.599	2.33	7.06	2.97	0.599	0.268	KURU	KURU
02	KURU	0.154	0.474	1.20	0.599	2.71	8.13	2.97	0.474	0.268	KURU	KURU
03	KURU	0.154	0.474	1.08	0.599	3.68	7.27	2.84	0.474	0.268	KURU	KURU
04	KURU	0.268	0.474	1.08	0.474	4.39	5.91	2.71	0.474	0.268	KURU	KURU
05	KURU	0.364	0.599	1.08	0.474	4.39	5.91	2.59	0.474	0.364	KURU	KURU
06	KURU	0.268	0.599	1.08	0.723	4.39	5.44	2.46	0.419	0.474	KURU	KURU
07	KURU	0.268	0.599	1.08	0.842	5.09	5.62	2.33	0.419	0.474	KURU	KURU
08	KURU	0.268	0.599	0.962	0.962	8.99	7.06	2.33	0.419	0.419	KURU	KURU
09	KURU	0.268	0.419	0.962	0.962	7.27	8.56	2.33	0.364	0.419	KURU	KURU
10	KURU	0.268	0.419	0.962	1.08	4.56	9.43	2.23	0.364	0.268	KURU	KURU
11	KURU	0.172	0.419	0.842	1.20	3.33	8.85	2.12	0.419	0.172	KURU	KURU
12	KURU	0.172	0.364	0.842	1.42	3.15	8.27	1.91	0.474	0.172	KURU	KURU
13	KURU	0.172	0.364	0.842	1.32	3.68	8.13	1.81	0.474	0.172	KURU	KURU
14	KURU	0.172	0.364	0.723	1.20	3.50	8.13	1.71	0.474	0.172	KURU	KURU
15	KURU	0.172	0.364	0.723	1.08	3.33	8.27	1.61	0.474	0.163	KURU	KURU
16	KURU	0.172	0.419	0.723	1.08	2.97	8.27	1.52	0.474	0.163	KURU	KURU
17	KURU	0.172	0.723	0.599	0.962	2.71	7.92	1.42	0.474	0.163	KURU	KURU
18	KURU	0.172	2.97	0.474	0.842	2.59	7.70	1.42	0.419	0.154	KURU	KURU
19	KURU	0.268	4.21	0.474	0.842	2.84	7.92	1.32	0.419	KURU	KURU	KURU
20	KURU	0.419	4.56	0.474	0.842	2.33	7.49	1.32	0.419	KURU	KURU	KURU
21	KURU	1.42	2.71	0.599	0.842	2.46	6.77	1.20	0.364	KURU	KURU	KURU
22	KURU	0.723	2.23	0.599	0.962	2.46	5.91	1.08	0.419	KURU	KURU	KURU
23	0.113	0.599	1.81	0.599	1.08	3.15	5.62	1.08	0.419	KURU	KURU	KURU
24	0.144	0.474	1.71	0.599	1.32	4.39	5.09	1.08	0.364	KURU	KURU	KURU
25	0.144	0.419	1.61	0.599	1.52	8.85	4.56	1.08	0.364	KURU	KURU	KURU
26	0.144	0.419	1.52	0.474	1.61	6.48	3.86	0.842	0.364	KURU	KURU	KURU
27	0.154	0.364	1.52	0.474	1.81	5.44	3.33	0.723	0.364	KURU	KURU	KURU
28	0.154	0.419	1.42	0.474	2.02	5.27	2.97	0.723	0.268	KURU	KURU	KURU
29	0.154	0.419	1.20	0.474	-----	5.27	2.84	0.723	0.364	KURU	KURU	KURU
30	0.154	0.474	1.20	0.474	-----	5.27	2.84	0.599	0.364	KURU	KURU	KURU
31	0.154	-----	1.20	0.599	-----	6.77	-----	0.599	-----	KURU	KURU	-----
Maks.	0.154	1.61	4.92	1.20	2.12	9.94	9.76	2.97	0.599	0.474	KURU	KURU
Min.	KURU	0.154	0.364	0.474	0.474	2.23	2.84	0.599	0.268	KURU	KURU	KURU
Ortalama	0.042	0.341	1.23	0.754	1.05	4.32	6.50	1.67	0.422	0.156	KURU	KURU
LT/SN/Km2	0.771	6.20	22.3	13.7	19.0	78.6	118.	30.3	7.67	2.83	0.000	0.000
AKIM mm.	2.07	16.1	59.7	36.7	46.0	211.	307.	81.1	19.9	7.57	0.000	0.000
MİL. M3	0.114	0.884	3.28	2.02	2.53	11.6	16.9	4.46	1.09	0.417	0.000	0.000

SU YILI (2006) YILLIK TOPLAM AKIM 43.30 MİLYON M3 787 MM. 24.9 LT/SN/Km2

20. Ceyhan Havzasi

D20A069 KARAPINAR D. GEBEN

YERİ : **K.MARAŞ-ANDIRIN-GEBEN KASABASINDAN SOLA AYRILAN YOLUN 7.KM.SİNDEDİR.**
36°23'20" Doğu - 37°45'30" Kuzey

YAĞIŞ ALANI : **31.50 km2** **YAKLAŞIK KOT : 1310 m**

GÖZLEM SÜRESİ : **15.05.1992 - 30.09.2006**

ORTALAMA AKIMLAR : **Gözlem süresinde 1.054 m3/sn. (13 Yıllık) 2006 Su yılında 1.036 m3/sn.**

ANLIK EN ÇOK VE EN AZ AKIMLAR:

2006 Su yılında anlık ençok akım	:	**8.02**	**m3/sn**	**10.04.2006**
2006 Su yılında anlık enaz akım	:	**0.160**	**m3/sn**	**05.10.2005**
Gözlem süresinde anlık ençok akım	:	**23.9**	**m3/sn**	**03.03.2005**
Gözlem süresinde anlık enaz akım	:	**0.160**	**m3/sn**	**29.12.2002**

Akımlar 01 Ekim 2005 'den 30 Eylül 2006' a kadar m3/sn olarak

Gün	Ekim	Kasım	Aralık	Ocak	Şubat	Mart	Nisan	Mayıs	Haziran	Temmuz	Ağustos	Eylül
01	0.220	0.160	0.220	0.370	0.320	1.22	4.90	2.08	0.980	0.614	0.370	0.320
02	0.220	0.220	0.220	0.370	0.320	1.47	5.50	1.96	0.980	0.492	0.370	0.320
03	0.220	0.160	0.220	0.320	0.320	2.08	5.30	1.96	0.858	0.492	0.370	0.320
04	0.160	0.220	0.220	0.370	0.320	2.39	4.90	1.83	0.858	0.492	0.370	0.320
05	0.160	0.220	0.220	0.492	0.320	2.08	4.90	1.83	0.858	0.492	0.370	0.270
06	0.160	0.160	0.220	0.492	0.370	2.08	4.90	1.71	0.858	0.492	0.370	0.270
07	0.160	0.160	0.220	0.492	0.370	2.39	4.90	1.71	0.858	0.492	0.370	0.270
08	0.160	0.160	0.220	0.370	0.492	4.50	5.30	1.59	0.858	0.370	0.370	0.270
09	0.160	0.160	0.220	0.370	0.492	4.30	6.34	1.59	0.858	0.370	0.370	0.270
10	0.160	0.160	0.220	0.370	0.492	3.15	7.30	1.47	0.736	0.370	0.370	0.270
11	0.160	0.160	0.220	0.370	0.614	2.58	7.06	1.47	0.736	0.370	0.370	0.270
12	0.160	0.160	0.220	0.370	0.614	2.20	6.34	1.35	0.736	0.492	0.370	0.270
13	0.160	0.160	0.160	0.370	0.492	2.20	5.90	1.47	0.736	0.492	0.320	0.270
14	0.160	0.160	0.160	0.370	0.370	2.39	5.70	1.47	0.736	0.492	0.370	0.270
15	0.160	0.160	0.220	0.370	0.614	2.58	5.70	1.35	0.736	0.492	0.370	0.270
16	0.220	0.160	0.220	0.370	0.614	2.39	5.70	1.35	0.736	0.492	0.370	0.270
17	0.220	0.160	0.270	0.370	0.614	2.20	5.70	1.35	0.736	0.492	0.370	0.270
18	0.220	0.160	2.08	0.370	0.614	2.20	4.90	1.22	0.614	0.492	0.370	0.270
19	0.220	0.270	2.39	0.370	0.492	2.20	4.30	1.22	0.614	0.492	0.370	0.270
20	0.220	0.614	2.39	0.370	0.370	2.08	3.91	1.22	0.614	0.492	0.320	0.220
21	0.160	0.270	1.59	0.370	0.370	2.08	3.72	1.22	0.614	0.492	0.320	0.220
22	0.160	0.220	0.858	0.492	0.492	2.08	3.34	1.22	0.614	0.492	0.320	0.220
23	0.160	0.220	0.736	0.492	0.492	2.39	3.15	1.22	0.614	0.492	0.320	0.220
24	0.160	0.220	0.614	0.492	0.492	2.96	2.96	1.10	0.614	0.492	0.320	0.220
25	0.160	0.220	0.492	0.492	0.736	5.50	2.58	1.10	0.614	0.492	0.320	0.220
26	0.160	0.220	0.492	0.492	0.858	4.50	2.39	1.10	0.492	0.492	0.320	0.270
27	0.160	0.220	0.370	0.370	0.980	3.91	2.08	1.10	0.492	0.492	0.320	0.270
28	0.160	0.220	0.370	0.320	1.10	3.72	2.20	0.980	0.614	0.492	0.320	0.270
29	0.160	0.220	0.370	0.320	-----	3.72	2.20	0.980	0.614	0.492	0.320	0.270
30	0.160	0.220	0.370	0.320	-----	3.91	2.08	0.980	0.614	0.492	0.320	0.220
31	0.160	-----	0.370	0.320	-----	4.30	-----	0.980	-----	0.492	0.320	-----
Maks.	0.220	0.858	3.15	0.492	1.10	7.54	8.02	2.20	2.39	0.736	0.492	0.320
Min.	0.160	0.160	0.160	0.320	0.220	0.320	1.96	0.980	0.492	0.370	0.320	0.220
Ortalama	0.175	0.206	0.554	0.393	0.527	2.83	4.54	1.39	0.720	0.480	0.349	0.265
LT/SN/Km2	5.57	6.55	17.6	12.5	16.7	89.9	144.	44.2	22.8	15.2	11.1	8.41
AKIM mm.	14.9	17.0	47.1	33.5	40.4	241.	373.	118.	59.2	40.8	29.7	21.8
MİL. M3	0.470	0.535	1.48	1.05	1.27	7.58	11.8	3.73	1.87	1.29	0.935	0.687

SU YILI (2006) YILLIK TOPLAM AKIM 32.70 MİLYON M3 1038 MM. 32.9 LT/SN/Km2

20. Ceyhan Havzasi

D20A071 KARAPINAR D. KIZILLAR KÖYÜ

YERİ : **ADANA İLİ KOZAN İLÇESİ KARAMEHMETLİ KÖYÜNDEDİR.**
35°42'31" Doğu - 37°30'50" Kuzey

YAĞIŞ ALANI : **49,70 km2** **YAKLAŞIK KOT : 235 m**

GÖZLEM SÜRESİ : **01.02.1995 - 30.09.2006**

ORTALAMA AKIMLAR : **Gözlem süresinde 0.747 m3/sn. (10 Yıllık) 2006 Su yılında 0.567 m3/sn.**

ANLIK EN ÇOK VE EN AZ AKIMLAR:

2006 Su yılında anlık ençok akım	**:**	**16.5**	**m3/sn**	**18.12.2005**
2006 Su yılında anlık enaz akım	**:**	**0.008**	**m3/sn**	**04.08.2006**
Gözlem süresinde anlık ençok akım	**:**	**185.**	**m3/sn**	**20.11.1995**
Gözlem süresinde anlık enaz akım	**:**	**0.000**	**m3/sn**	**01.12.1991**

Akımlar 01 Ekim 2005 'den 30 Eylül 2006' a kadar m3/sn olarak

Gün	Ekim	Kasım	Aralık	Ocak	Şubat	Mart	Nisan	Mayıs	Haziran	Temmuz	Ağustos	Eylül
01	0.075	0.147	0.064	0.565	0.565	0.934	0.707	0.208	0.165	0.046	0.026	0.019
02	0.075	0.147	0.054	0.565	0.565	0.934	0.707	0.208	0.165	0.046	0.026	0.015
03	0.106	0.147	0.054	0.445	0.565	1.67	0.605	0.165	0.165	0.046	0.026	0.019
04	0.106	0.565	0.054	0.385	0.505	2.71	0.605	0.165	0.165	0.046	0.015	0.019
05	0.106	0.445	0.054	0.385	0.505	1.67	0.605	0.165	0.165	0.046	0.015	0.019
06	0.147	0.267	0.054	0.385	0.505	1.26	0.605	0.251	0.103	0.046	0.015	0.015
07	0.147	0.267	0.054	0.346	0.892	1.26	0.503	0.208	0.103	0.046	0.019	0.015
08	0.147	0.188	0.054	0.346	5.58	1.67	0.503	0.208	0.072	0.046	0.019	0.012
09	0.147	0.168	0.054	0.306	3.71	3.60	0.503	0.208	0.072	0.046	0.026	0.015
10	0.188	0.127	0.054	0.306	2.58	3.12	0.503	0.208	0.072	0.033	0.026	0.015
11	0.188	0.127	0.043	0.306	4.51	2.50	0.503	0.208	0.059	0.033	0.015	0.015
12	0.188	0.127	0.043	0.306	5.32	2.50	0.503	0.208	0.059	0.033	0.015	0.012
13	0.267	0.127	0.043	0.306	6.34	2.30	0.401	0.165	0.059	0.033	0.015	0.015
14	0.306	0.127	0.043	0.267	5.52	2.09	0.401	0.165	0.059	0.033	0.015	0.015
15	0.306	0.127	0.064	0.267	4.97	1.88	0.401	0.251	0.046	0.033	0.019	0.015
16	0.306	0.127	0.106	0.267	4.15	1.88	0.326	0.251	0.046	0.033	0.015	0.015
17	0.505	0.127	6.93	0.267	4.15	1.67	0.326	0.208	0.072	0.033	0.015	0.015
18	0.306	0.127	9.62	0.267	2.50	3.33	0.326	0.208	0.059	0.033	0.015	0.015
19	0.445	0.127	6.12	0.267	1.88	3.60	0.326	0.326	0.059	0.033	0.015	0.015
20	0.267	0.127	2.41	0.505	1.67	2.30	0.326	0.251	0.059	0.033	0.019	0.015
21	0.227	0.127	1.20	0.445	1.47	1.88	0.326	0.165	0.059	0.033	0.015	0.103
22	0.188	0.106	0.996	0.385	1.26	1.47	0.326	0.208	0.059	0.033	0.012	0.133
23	0.168	0.086	0.996	0.385	1.10	1.10	0.251	0.133	0.059	0.033	0.019	0.072
24	0.168	0.075	0.892	0.385	1.10	1.10	1.26	0.103	0.059	0.046	0.012	0.059
25	0.168	0.075	0.789	0.789	0.934	1.47	0.605	0.103	0.059	0.033	0.012	0.046
26	0.168	0.075	0.685	1.62	0.934	1.10	0.326	0.103	0.059	0.033	0.012	0.026
27	0.147	0.064	0.685	1.31	1.10	1.10	0.251	0.133	0.059	0.019	0.015	0.026
28	0.147	0.064	0.625	0.996	1.26	0.934	0.251	0.133	0.059	0.033	0.015	0.026
29	0.147	0.064	0.625	0.789	-----	0.934	0.208	0.133	0.046	0.019	0.015	0.026
30	0.147	0.064	0.625	0.625	-----	0.821	0.208	0.208	0.046	0.019	0.019	0.026
31	0.147	-----	0.565	0.625	-----	0.821	-----	0.165	-----	0.019	0.015	-----
Maks.	2.58	3.44	16.5	2.75	7.44	6.34	6.07	0.707	0.208	0.059	0.033	3.12
Min.	0.075	0.054	0.043	0.227	0.505	0.707	0.208	0.046	0.019	0.012	0.008	0.008
Ortalama	0.198	0.151	1.12	0.497	2.36	1.79	0.457	0.188	0.080	0.035	0.017	0.028
LT/SN/Km2	3.99	3.04	22.5	10.0	47.5	36.1	9.19	3.78	1.60	0.712	0.345	0.572
AKIM mm.	10.7	7.89	60.2	26.8	115.	96.7	23.8	10.1	4.15	1.91	0.925	1.48
MİL. M3	0.531	0.392	2.99	1.33	5.71	4.80	1.18	0.503	0.206	0.095	0.046	0.074

SU YILI (2006) YILLIK TOPLAM AKIM 17.86 MİLYON M3 359 MM. 11.4 LT/SN/Km2

20. Ceyhan Havzasi

D20A072 MELETMEZ D. ACARMANTAŞ

YERİ : **ADANA İLİ KOZAN İLÇESİ ACARMANTAŞ KÖYÜ YAKINLARINDADIR.**
35°55'22" Doğu - 37°29'13" Kuzey

YAĞIŞ ALANI : **48,80 km2** **YAKLAŞIK KOT : 100 m**

GÖZLEM SÜRESİ : **01.06.1992 - 30.09.2006**

ORTALAMA AKIMLAR : **Gözlem süresinde 0.365 m3/sn. (11 Yıllık) 2006 Su yılında 0.189 m3/sn.**

ANLIK EN ÇOK VE EN AZ AKIMLAR:

2006 Su yılında anlık ençok akım	**:**	**3.71**	**m3/sn**	**08.02.2006**
2006 Su yılında anlık enaz akım	**:**	**0.000**	**m3/sn**	**14.01.2006**
Gözlem süresinde anlık ençok akım	**:**	**66.6**	**m3/sn**	**30.05.2003**
Gözlem süresinde anlık enaz akım	**:**	**0.000**	**m3/sn**	**10.08.1994**

Akımlar 01 Ekim 2005 'den 30 Eylül 2006' a kadar m3/sn olarak

Gün	Ekim	Kasım	Aralık	Ocak	Şubat	Mart	Nisan	Mayıs	Haziran	Temmuz	Ağustos	Eylül
01	0.037	0.051	0.028	0.065	0.037	0.369	0.810	0.234	0.051	0.051	KURU	KURU
02	0.037	0.051	0.028	0.065	0.037	0.369	0.739	0.166	0.051	0.051	KURU	KURU
03	0.037	0.051	0.028	0.065	0.037	0.369	0.739	0.166	0.085	0.051	KURU	KURU
04	0.037	0.065	0.019	0.051	0.037	0.369	0.606	0.166	0.065	0.051	KURU	KURU
05	0.037	0.065	0.019	0.051	0.037	0.320	0.606	0.166	0.051	KURU	KURU	KURU
06	0.037	0.065	0.019	0.037	0.037	0.320	0.606	0.136	0.051	KURU	KURU	KURU
07	0.085	0.065	0.019	0.028	0.136	0.320	0.606	0.166	0.051	KURU	KURU	KURU
08	0.065	0.065	0.019	0.028	1.45	0.369	0.539	0.166	0.037	KURU	KURU	KURU
09	0.065	0.085	0.019	0.028	0.882	0.882	0.539	0.166	0.037	KURU	KURU	KURU
10	0.065	0.085	0.019	0.028	0.539	0.739	0.539	0.105	0.065	KURU	KURU	KURU
11	0.065	0.085	0.019	0.028	0.882	0.673	0.539	0.105	0.065	0.028	KURU	KURU
12	0.065	0.085	0.019	0.028	1.05	0.673	0.539	0.105	0.051	KURU	KURU	KURU
13	0.136	0.085	0.019	0.019	1.90	0.673	0.539	0.105	0.051	KURU	KURU	KURU
14	0.085	0.136	0.019	0.019	1.67	0.673	0.476	0.085	0.051	KURU	KURU	KURU
15	0.085	0.136	0.019	0.019	1.55	0.606	0.476	0.085	0.051	KURU	KURU	KURU
16	0.065	0.136	0.105	0.019	1.15	0.606	0.476	0.085	0.051	KURU	KURU	KURU
17	0.065	0.166	0.065	0.019	0.953	0.606	0.476	0.065	0.051	0.019	KURU	KURU
18	0.065	0.197	0.234	0.019	0.810	0.882	0.413	0.065	0.051	0.028	KURU	KURU
19	0.065	0.270	0.882	0.019	0.739	1.15	0.413	0.065	0.051	0.234	KURU	KURU
20	0.065	0.085	0.136	0.085	0.673	1.05	0.413	0.085	0.037	KURU	KURU	KURU
21	0.065	0.085	0.085	0.037	0.606	1.05	0.369	0.085	0.037	KURU	KURU	KURU
22	0.065	0.065	0.085	0.037	0.539	1.05	0.369	0.085	0.037	0.051	KURU	KURU
23	0.065	0.065	0.065	0.037	0.476	0.953	0.369	0.065	0.037	KURU	KURU	KURU
24	0.085	0.065	0.065	0.037	0.476	0.882	0.320	0.065	0.037	KURU	KURU	KURU
25	0.085	0.065	0.065	0.037	0.413	1.05	0.320	0.065	0.037	KURU	KURU	KURU
26	0.085	0.065	0.065	0.051	0.369	1.05	0.320	0.065	0.051	KURU	KURU	KURU
27	0.085	0.065	0.065	0.051	0.369	1.05	0.270	0.065	0.136	KURU	KURU	KURU
28	0.085	0.065	0.065	0.037	0.369	1.05	0.270	0.065	0.051	KURU	KURU	KURU
29	0.085	0.037	0.065	0.037	-----	0.953	0.270	0.051	0.051	KURU	KURU	KURU
30	0.051	0.037	0.065	0.037	-----	0.953	0.234	0.051	0.051	KURU	KURU	KURU
31	0.051	-----	0.065	0.037	-----	0.953	-----	0.051	-----	KURU	KURU	-----
Maks.	0.539	0.882	2.86	0.234	3.71	3.57	0.953	0.320	0.539	0.810	KURU	KURU
Min.	0.028	0.028	0.019	KURU	0.037	0.270	0.166	0.037	0.028	KURU	KURU	KURU
Ortalama	0.067	0.088	0.080	0.037	0.651	0.742	0.473	0.103	0.053	0.018	KURU	KURU
LT/SN/Km2	1.37	1.81	1.65	0.763	13.3	15.2	9.70	2.12	1.08	0.373	0.000	0.000
AKIM mm.	3.66	4.68	4.41	2.04	32.3	40.7	25.1	5.67	2.80	0.999	0.000	0.000
MİL. M3	0.179	0.228	0.215	0.100	1.57	1.99	1.23	0.276	0.136	0.049	0.000	0.000

SU YILI (2006) YILLIK TOPLAM AKIM 5.97 MİLYON M3 122 MM. 3.9 LT/SN/Km2

20. Ceyhan Havzasi

D20A073 HASANBEYLİ D. HASANBEYLİ

YERİ : **OSMANİYE İLİ HASANBEYLİ İLÇESİ YAKINLARINDADIR.**
36°32'43" Doğu - 37°7'46" Kuzey

YAĞIŞ ALANI : **23,40 km2** **YAKLAŞIK KOT : 730 m**

GÖZLEM SÜRESİ : **01.01.1996 - 30.09.2006**

ORTALAMA AKIMLAR : **Gözlem süresinde 0.284 m3/sn. (7 Yıllık) 2006 Su yılında 0.194 m3/sn.**

ANLIK EN ÇOK VE EN AZ AKIMLAR:

2006 Su yılında anlık ençok akım	**:**	**0.943 m3/sn**	**08.02.2006**
2006 Su yılında anlık enaz akım	**:**	**0.038 m3/sn**	**19.06.2006**
Gözlem süresinde anlık ençok akım	**:**	**4.6 m3/sn**	**07.03.1996**
Gözlem süresinde anlık enaz akım	**:**	**0.016 m3/sn**	**23.07.2005**

Akımlar 01 Ekim 2005 'den 30 Eylül 2006' a kadar m3/sn olarak

Gün	Ekim	Kasım	Aralık	Ocak	Şubat	Mart	Nisan	Mayıs	Haziran	Temmuz	Ağustos	Eylül
01	0.065	0.186	0.138	0.162	0.227	0.510	0.270	0.302	0.186	0.080	0.050	0.065
02	0.065	0.138	0.138	0.162	0.227	0.510	0.270	0.302	0.162	0.080	0.050	0.080
03	0.065	0.138	0.138	0.162	0.227	0.510	0.270	0.302	0.162	0.080	0.038	0.080
04	0.065	0.138	0.138	0.162	0.227	0.510	0.270	0.302	0.162	0.100	0.038	0.065
05	0.065	0.162	0.138	0.162	0.227	0.510	0.254	0.270	0.113	0.100	0.050	0.065
06	0.065	0.162	0.138	0.162	0.227	0.510	0.270	0.270	0.113	0.080	0.050	0.065
07	0.065	0.162	0.138	0.162	0.418	0.510	0.270	0.270	0.113	0.080	0.038	0.080
08	0.065	0.162	0.207	0.162	0.650	0.510	0.302	0.270	0.113	0.065	0.050	0.080
09	0.065	0.162	0.186	0.162	0.510	0.510	0.302	0.254	0.113	0.050	0.050	0.065
10	0.065	0.162	0.162	0.162	0.449	0.545	0.302	0.254	0.100	0.050	0.050	0.065
11	0.065	0.113	0.162	0.162	0.449	0.545	0.328	0.254	0.100	0.080	0.050	0.050
12	0.065	0.113	0.162	0.162	0.449	0.545	0.328	0.254	0.100	0.050	0.050	0.050
13	0.065	0.113	0.162	0.162	0.580	0.545	0.328	0.254	0.100	0.038	0.050	0.050
14	0.065	0.113	0.162	0.162	0.580	0.545	0.328	0.254	0.080	0.038	0.050	0.050
15	0.065	0.113	0.162	0.162	0.545	0.545	0.328	0.254	0.100	0.038	0.065	0.050
16	0.065	0.138	0.162	0.162	0.545	0.479	0.328	0.227	0.080	0.050	0.065	0.080
17	0.065	0.138	0.162	0.162	0.545	0.449	0.328	0.227	0.065	0.050	0.050	0.065
18	0.100	0.138	0.162	0.162	0.545	0.449	0.302	0.227	0.065	0.050	0.050	0.065
19	0.186	0.138	0.162	0.162	0.545	0.580	0.302	0.227	0.050	0.050	0.038	0.065
20	0.186	0.138	0.162	0.207	0.545	0.510	0.302	0.227	0.038	0.050	0.038	0.065
21	0.162	0.138	0.162	0.207	0.545	0.510	0.302	0.227	0.038	0.050	0.038	0.080
22	0.162	0.138	0.162	0.207	0.545	0.479	0.270	0.207	0.038	0.050	0.038	0.080
23	0.162	0.138	0.162	0.207	0.545	0.449	0.270	0.207	0.050	0.050	0.065	0.113
24	0.162	0.138	0.162	0.207	0.545	0.449	0.270	0.207	0.065	0.065	0.050	0.138
25	0.162	0.138	0.162	0.254	0.545	0.449	0.270	0.207	0.065	0.038	0.050	0.162
26	0.162	0.138	0.162	0.254	0.510	0.418	0.270	0.207	0.050	0.038	0.050	0.162
27	0.162	0.138	0.162	0.227	0.510	0.418	0.270	0.207	0.100	0.038	0.065	0.113
28	0.162	0.138	0.162	0.227	0.510	0.357	0.270	0.186	0.100	0.038	0.065	0.113
29	0.162	0.138	0.162	0.227	-----	0.357	0.270	0.186	0.100	0.050	0.065	0.100
30	0.162	0.138	0.162	0.254	-----	0.357	0.254	0.186	0.100	0.038	0.065	0.100
31	0.186	-----	0.162	0.227	-----	0.357	-----	0.186	-----	0.038	0.065	-----
Maks.	0.227	0.254	0.207	0.270	0.943	0.737	0.357	0.357	0.207	0.270	0.080	0.186
Min.	0.065	0.080	0.138	0.162	0.227	0.162	0.254	0.162	0.038	0.038	0.038	0.050
Ortalama	0.109	0.140	0.159	0.187	0.463	0.482	0.290	0.239	0.094	0.057	0.051	0.082
LT/SN/Km2	4.66	5.99	6.79	7.97	19.8	20.6	12.4	10.2	4.02	2.42	2.19	3.51
AKIM mm.	12.5	15.5	18.2	21.4	47.9	55.1	32.1	27.4	10.4	6.47	5.86	9.09
MİL. M3	0.292	0.363	0.425	0.500	1.12	1.29	0.752	0.641	0.244	0.151	0.137	0.213

SU YILI (2006) YILLIK TOPLAM AKIM 6.13 MİLYON M3 262 MM. 8.3 LT/SN/Km2

22
DOĞU KARADENİZ HAVZASI

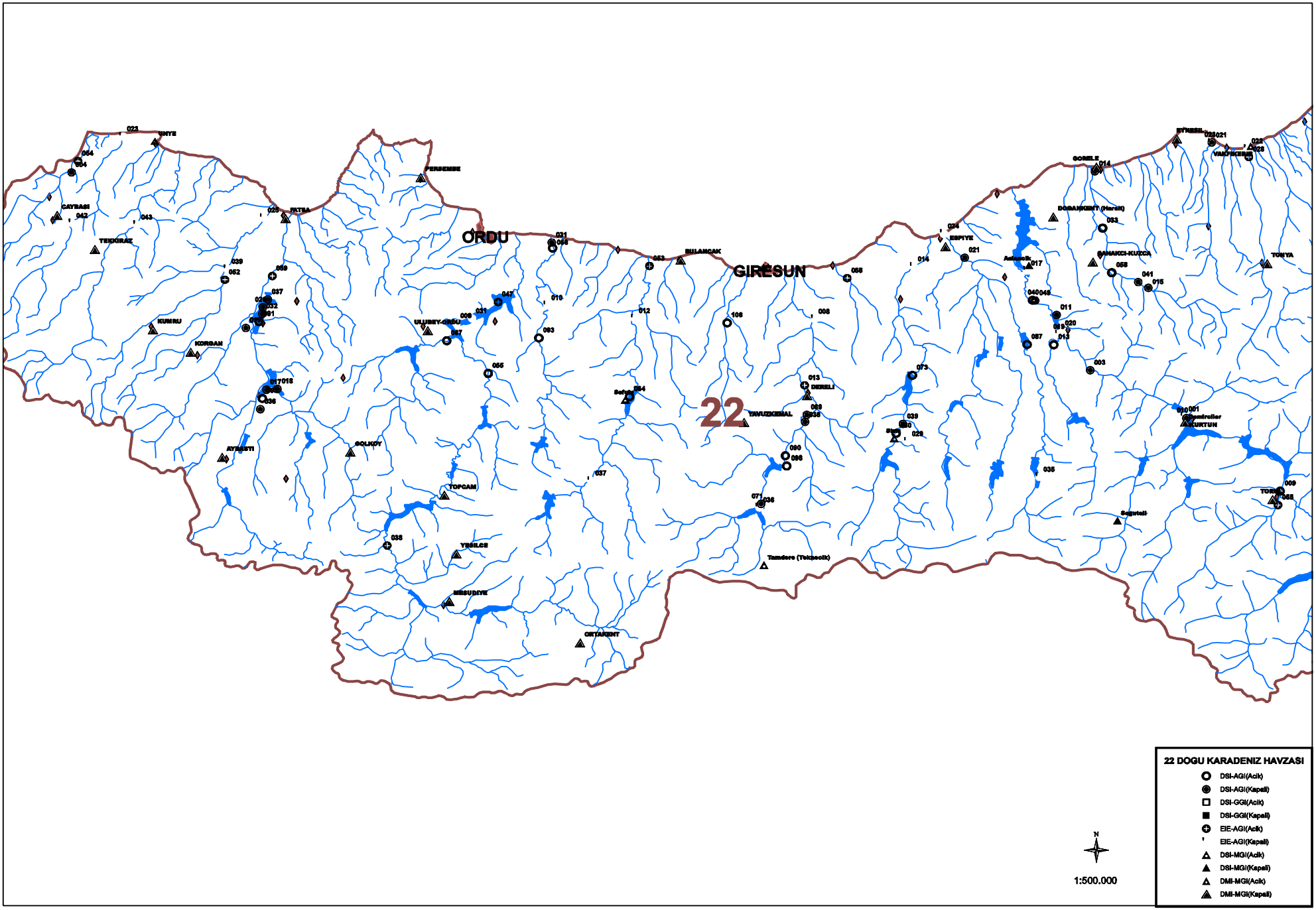
ORDU
GIRESUN
22
UNYE
PERSEMBE
FATSA
CAYBASI
TEKKIRAZ
KUMRU
KORGAN
ULUBEY-ORDU
BULANCAK
YAVUZKEMAL
DERELI
ESPIYE
GORELE
DOGANKENT (Harsit)
BANAKCI-KUZCA
TONYA
TORUL
KURTUN
Şebinkarahisar
Şiranli
AYBASTI
GOLKOY
TOPCAM
YEMILCE
MESUDIYE
ORTAKENT
Tamdere (Tokbeolik)
1:500.000
N
22 DOGU KARADENIZ HAVZASI
DSI-AGI(Acik)
DSI-AGI(Kapali)
DSI-GGI(Acik)
DSI-GGI(Kapali)
EIE-AGI(Acik)
EIE-AGI(Kapali)
DSI-MGI(Acik)
DSI-MGI(Kapali)
DMI-MGI(Acik)
DMI-MGI(Kapali)

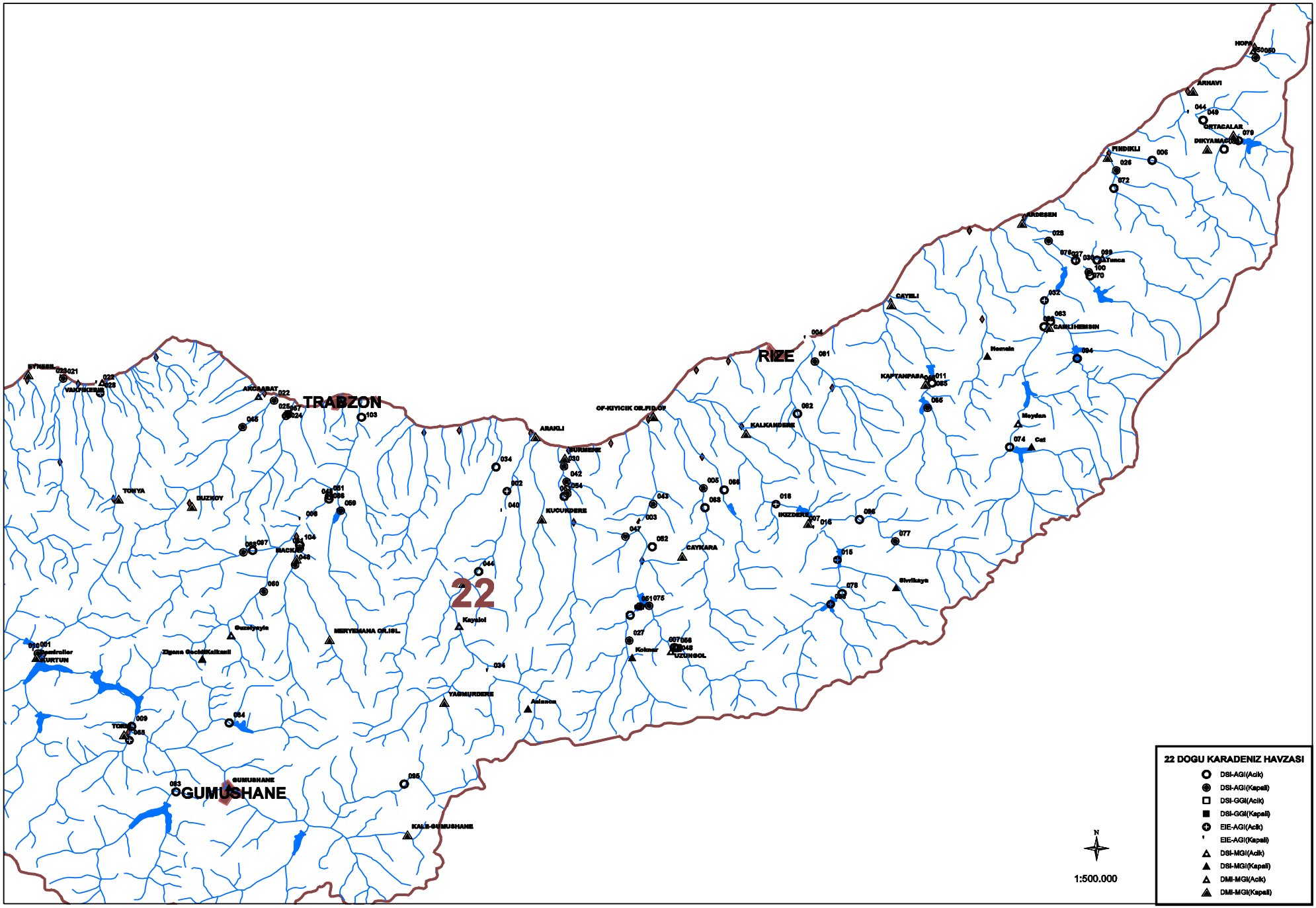
22
TRABZON
RIZE
GUMUSHANE
22 DOGU KARADENIZ HAVZASI
DSI-AGI(Acik)
DSI-AGI(Kapali)
DSI-GGI(Acik)
DSI-GGI(Kapali)
EIE-AGI(Acik)
EIE-AGI(Kapali)
DSI-MGI(Acik)
DSI-MGI(Kapali)
DMI-MGI(Acik)
DMI-MGI(Kapali)
N
1:500.000

22. Dogu Karadeniz Havzasi

D22A006 ABUCAĞLAYAN D. KÖPRÜBAŞI

YERİ : **FINDIKLI - ARHAVİ SAHIL YOLUNDA FINDIKLI ÇIKIŞINDA SAĞA AYRILAN ÇAĞLAYAN KÖYÜ 4 KM SINDEKI KÖPRÜDEDIR.**
41°15'30" Doğu - 41°13'51" Kuzey

YAĞIŞ ALANI : **156,00 km2** **YAKLAŞIK KOT : 60 m**

GÖZLEM SÜRESİ : **01.10.1965 - 30.09.2006**

ORTALAMA AKIMLAR : **Gözlem süresinde 9.040 m3/sn. (34 Yıllık) 2006 Su yılında 9.442 m3/sn.**

ANLIK EN ÇOK VE EN AZ AKIMLAR:

2006 Su yılında anlık ençok akım	:	**107.**	**m3/sn**	**04.07.2006**
2006 Su yılında anlık enaz akım	:	**1.50**	**m3/sn**	**01.09.2006**
Gözlem süresinde anlık ençok akım	:	**350.**	**m3/sn**	**03.09.1997**
Gözlem süresinde anlık enaz akım	:	**0.720**	**m3/sn**	**23.10.1991**

Akımlar 01 Ekim 2005 'den 30 Eylül 2006' a kadar m3/sn olarak

Gün	Ekim	Kasım	Aralık	Ocak	Şubat	Mart	Nisan	Mayıs	Haziran	Temmuz	Ağustos	Eylül
01	5.44	16.2	17.9	3.16	2.16	10.2	7.80	14.2	19.3	10.2	8.10	1.72
02	4.08	16.2	10.2	4.88	2.16	10.2	8.10	13.0	20.2	22.5	6.90	2.16
03	2.16	13.8	12.2	3.56	2.16	13.0	12.6	15.4	20.6	23.5	6.00	2.88
04	1.94	13.4	14.6	3.16	2.38	11.8	10.2	17.0	19.7	46.3	5.44	6.30
05	9.40	11.0	9.80	3.02	2.38	13.4	10.2	15.4	18.4	28.0	4.88	10.6
06	9.80	11.4	7.20	3.02	2.38	9.00	7.80	16.2	17.5	19.7	4.60	8.10
07	9.40	11.0	6.30	5.16	4.08	10.2	6.90	19.7	17.9	19.3	4.08	18.4
08	9.80	9.40	5.44	3.56	8.40	10.2	7.80	22.0	22.0	19.3	3.82	21.1
09	9.40	33.2	4.88	5.72	6.90	13.4	7.80	19.7	17.0	24.5	3.56	7.20
10	9.40	20.2	4.34	7.20	6.90	16.2	11.8	18.8	15.4	16.6	4.60	4.34
11	9.40	13.4	4.34	4.88	6.90	11.4	15.4	16.2	13.4	13.0	3.82	3.30
12	9.40	15.8	4.08	3.56	8.40	7.80	15.4	15.0	12.6	11.0	3.30	3.02
13	9.40	26.5	4.34	3.16	8.40	7.80	17.5	16.6	18.4	9.80	3.16	6.60
14	9.40	14.6	4.08	3.02	6.90	7.80	15.4	18.4	13.4	8.70	3.16	11.4
15	9.40	11.4	3.82	3.56	5.44	8.40	16.2	23.0	12.2	8.70	3.02	5.44
16	9.40	9.80	3.56	3.56	4.08	10.2	16.2	16.6	11.0	11.8	3.02	9.40
17	9.40	9.40	4.88	3.02	2.38	9.00	17.0	16.2	10.2	8.70	2.88	9.40
18	9.40	7.80	4.60	2.88	2.38	7.20	17.9	20.2	11.4	7.50	2.74	8.10
19	9.40	7.20	3.82	2.74	2.38	6.30	13.4	17.9	12.2	7.80	2.74	5.16
20	9.40	6.30	3.30	2.60	10.2	6.90	12.6	16.6	11.4	11.4	5.72	3.56
21	9.40	6.00	5.16	3.82	6.30	8.40	12.2	17.9	9.40	11.8	4.60	3.02
22	9.80	6.60	5.16	2.74	5.44	6.90	13.8	19.7	9.00	10.2	3.56	2.88
23	9.40	8.70	4.08	3.56	5.44	6.90	18.4	19.3	8.70	9.00	3.16	3.56
24	9.40	9.00	3.56	3.16	5.44	6.90	15.4	18.4	8.40	8.10	2.74	3.16
25	9.40	7.50	3.56	3.02	6.90	11.8	14.2	18.4	8.10	7.80	2.60	3.30
26	9.40	6.90	3.82	2.60	6.90	11.8	18.4	21.1	8.10	7.20	2.60	2.74
27	9.40	8.40	4.08	2.60	7.80	10.2	19.7	22.0	8.10	6.30	2.38	8.40
28	9.80	9.40	3.56	2.74	10.2	7.50	14.2	21.1	9.00	6.30	2.16	10.6
29	9.40	10.6	3.16	2.88	-----	6.90	9.80	19.3	9.00	7.20	2.16	4.88
30	9.40	7.20	3.16	2.60	-----	6.90	9.40	15.8	9.00	14.2	1.94	3.30
31	9.40	-----	3.16	2.38	-----	6.90	-----	17.5	-----	13.0	1.94	-----
Maks.	10.6	47.6	21.5	8.10	15.8	24.0	24.5	29.5	27.0	107.	35.4	32.1
Min.	1.94	5.72	2.88	2.16	2.16	6.30	6.60	10.2	7.80	6.00	1.72	1.50
Ortalama	8.68	11.9	5.68	3.47	5.42	9.40	13.1	18.0	13.4	13.9	3.72	6.47
LT/SN/Km2	55.6	76.6	36.4	22.2	34.7	60.3	84.1	116.	85.7	88.8	23.9	41.5
AKIM mm.	149.	198.	97.6	59.5	84.1	161.	218.	309.	222.	238.	63.9	107.
MİL. M3	23.2	31.0	15.2	9.29	13.1	25.2	34.0	48.3	34.6	37.1	9.97	16.8

SU YILI (2006) YILLIK TOPLAM AKIM 297.76 MİLYON M3 1909 MM. 60.5 LT/SN/Km2

22. Dogu Karadeniz Havzasi

D22A007 HALDİZEN S. ŞERAH

YERİ : **TARBZON RİZE YOLUNDAN OF İLÇESİ GİRİŞİNDE SAĞA AYRILAN ÇAYKARA YOLUNU TAKİBEN UZUNGÖL BELDESİ GİRİŞİNDEDİR.**
40°17'20" Doğu - 40°37'20" Kuzey

YAĞIŞ ALANI : **154,70 km2** **YAKLAŞIK KOT : 1114 m**

GÖZLEM SÜRESİ : **18.08.1965 - 30.09.2006**

ORTALAMA AKIMLAR : **Gözlem süresinde 4.294 m3/sn. (36 Yıllık) 2006 Su yılında 4.216 m3/sn.**

ANLIK EN ÇOK VE EN AZ AKIMLAR:

2006 Su yılında anlık ençok akım	:	**22.0**	**m3/sn**	**07.05.2006**
2006 Su yılında anlık enaz akım	:	**0.420**	**m3/sn**	**03.09.2006**
Gözlem süresinde anlık ençok akım	:	**57.2**	**m3/sn**	**28.04.1990**
Gözlem süresinde anlık enaz akım	:	**0.350**	**m3/sn**	**28.01.1984**

Akımlar 01 Ekim 2005 'den 30 Eylül 2006' a kadar m3/sn olarak

Gün	Ekim	Kasım	Aralık	Ocak	Şubat	Mart	Nisan	Mayıs	Haziran	Temmuz	Ağustos	Eylül
01	1.93	12.5	3.95	1.32	0.910	2.95	3.25	8.30	13.6	5.44	2.55	0.420
02	1.77	9.40	3.59	1.32	0.910	2.95	4.18	11.0	13.3	5.62	2.27	0.420
03	1.93	8.14	3.41	1.17	0.910	2.95	4.00	14.4	12.9	6.34	2.14	0.420
04	1.93	7.42	3.59	1.17	0.910	3.10	3.40	12.7	13.1	5.08	1.93	0.540
05	5.20	6.88	3.41	1.17	0.910	3.10	3.55	12.1	12.5	4.54	1.79	0.660
06	4.46	6.88	3.41	1.32	0.910	2.55	3.70	13.8	12.9	4.72	1.56	0.660
07	4.12	6.52	3.41	1.61	0.910	2.55	3.70	18.0	14.0	4.90	1.47	0.660
08	3.95	6.52	3.23	1.45	0.910	2.80	4.00	18.4	12.3	8.10	1.36	0.660
09	3.59	7.24	3.23	1.45	0.910	5.26	3.10	15.5	10.4	6.70	1.15	0.660
10	3.23	6.88	3.23	1.17	0.910	5.08	5.98	12.5	9.75	5.08	1.05	0.540
11	2.89	6.16	3.05	1.04	0.910	3.10	5.08	10.8	8.50	4.54	0.900	0.540
12	2.73	5.20	3.05	1.04	1.17	2.40	7.30	10.8	8.50	4.36	0.810	0.540
13	2.41	4.80	2.89	1.04	1.45	1.93	8.10	11.4	7.50	4.36	0.780	0.660
14	2.09	4.46	3.05	1.04	1.17	2.14	8.50	11.0	8.10	4.18	0.780	0.660
15	2.41	4.29	3.05	1.04	1.04	2.80	10.4	9.12	7.10	4.00	0.780	0.660
16	2.89	3.95	2.89	1.04	0.910	2.80	11.9	9.12	5.80	3.55	0.660	0.780
17	9.94	3.77	2.89	1.04	0.910	1.93	8.50	10.4	6.52	2.95	0.660	0.780
18	9.58	3.59	2.73	1.04	0.910	2.04	7.90	11.0	6.34	2.80	0.660	0.660
19	8.68	3.23	2.73	1.04	1.04	1.93	7.10	8.91	5.80	2.80	1.17	0.420
20	8.86	2.73	2.73	1.04	1.04	1.93	7.90	9.12	5.44	3.10	1.93	0.420
21	7.96	2.57	2.57	0.910	0.910	1.79	9.54	10.4	5.98	3.10	1.77	0.420
22	6.88	2.73	1.93	0.910	1.04	1.56	8.91	11.2	5.80	3.10	1.61	0.420
23	6.16	2.73	1.77	1.04	1.32	1.56	8.30	11.4	5.44	3.10	1.45	0.660
24	5.80	2.41	1.77	0.910	1.61	1.47	11.6	11.0	5.44	3.10	1.32	0.540
25	5.80	2.25	1.61	0.910	2.09	2.65	10.6	12.7	5.08	2.80	1.17	0.540
26	6.34	2.25	1.45	1.45	1.93	3.55	8.10	14.0	5.62	2.80	1.04	0.540
27	6.70	2.25	1.45	1.04	2.14	3.25	6.52	13.8	5.08	2.80	0.910	0.540
28	6.34	2.73	1.45	0.910	2.04	2.55	5.80	12.5	5.44	2.65	0.780	0.540
29	7.06	3.23	1.45	0.910	-----	2.27	5.26	9.54	5.08	2.65	0.660	0.540
30	6.70	3.77	1.32	0.910	-----	2.40	8.70	10.2	4.90	2.65	0.660	0.420
31	9.58	-----	1.32	0.910	-----	2.80	-----	12.7	-----	2.55	0.540	-----
Maks.	17.3	16.4	4.12	1.61	2.14	6.90	14.4	22.0	16.6	9.54	2.55	0.780
Min.	1.77	2.25	1.17	0.910	0.910	1.47	3.10	7.70	4.18	2.55	0.540	0.420
Ortalama	5.16	4.92	2.63	1.11	1.17	2.65	6.83	11.9	8.27	4.01	1.24	0.564
LT/SN/Km2	33.3	31.8	17.0	7.16	7.56	17.1	44.1	76.7	53.5	26.0	7.99	3.65
AKIM mm.	89.3	82.4	45.6	19.2	18.3	45.9	114.	205.	139.	69.5	21.4	9.45
MİL. M3	13.8	12.7	7.05	2.97	2.83	7.10	17.7	31.8	21.4	10.8	3.31	1.46

SU YILI (2006) YILLIK TOPLAM AKIM 132.92 MİLYON M3 859 MM. 27.3 LT/SN/Km2

22. Dogu Karadeniz Havzasi

D22A009 Harsit Ç. Torul

YERİ : **TORUL İLÇESİNDEKİ BETON KÖPRÜNÜN MENBAĞINDADIR.**
39°17'50" Doğu - 40°33'30" Kuzey

YAĞIŞ ALANI : **1900,00 km2** **YAKLAŞIK KOT : 925 m**

GÖZLEM SÜRESİ : **21.06.1966 - 30.09.2006**

ORTALAMA AKIMLAR : **Gözlem süresinde 16.479 m3/sn. (33 Yıllık) 2006 Su yılında 24.035 m3/sn.**

ANLIK EN ÇOK VE EN AZ AKIMLAR:

2006 Su yılında anlık ençok akım	:	**179.**	**m3/sn**	**25.04.2006**
2006 Su yılında anlık enaz akım	:	**1.33**	**m3/sn**	**02.10.2005**
Gözlem süresinde anlık ençok akım	:	**629.**	**m3/sn**	**20.06.1990**
Gözlem süresinde anlık enaz akım	:	**0.800**	**m3/sn**	**14.08.1974**

Akımlar 01 Ekim 2005 'den 30 Eylül 2006' a kadar m3/sn olarak

Gün	Ekim	Kasım	Aralık	Ocak	Şubat	Mart	Nisan	Mayıs	Haziran	Temmuz	Ağustos	Eylül
01	1.58	93.3	14.4	3.52	3.10	18.7	65.5	167.	32.0	10.9	1.89	2.43
02	1.33	61.0	12.6	4.78	3.52	19.4	65.5	126.	32.0	7.00	1.89	2.43
03	1.58	47.0	12.0	4.57	3.31	22.2	78.2	133.	31.3	6.10	2.02	2.43
04	4.57	37.0	12.6	4.57	3.31	24.3	88.7	157.	30.6	5.50	2.16	2.43
05	2.83	30.6	12.6	4.57	3.52	41.0	87.5	136.	27.1	4.78	2.43	2.43
06	1.89	29.9	11.6	4.36	3.52	32.0	77.1	118.	24.3	4.15	2.43	2.43
07	1.67	27.1	10.5	4.57	4.15	29.9	71.3	126.	22.9	4.15	2.56	2.56
08	1.50	25.7	9.72	4.78	4.99	32.0	62.0	114.	22.9	4.57	2.70	2.56
09	1.42	23.6	8.96	4.78	4.99	46.0	60.0	130.	24.3	5.20	2.97	2.56
10	1.33	20.1	8.58	4.78	6.70	77.1	66.6	130.	20.8	5.20	3.10	2.56
11	1.33	18.0	7.90	4.57	8.20	66.6	104.	108.	17.4	4.57	3.10	2.56
12	1.42	16.8	7.60	4.15	8.20	54.0	117.	92.2	13.8	4.15	3.10	2.56
13	1.42	14.4	7.00	3.94	7.90	44.0	122.	80.6	11.6	3.94	2.70	2.97
14	1.42	12.0	6.40	3.94	8.20	37.0	119.	79.4	10.5	3.31	2.43	3.52
15	1.67	11.2	6.10	3.94	8.20	33.0	114.	78.2	9.34	3.10	2.70	3.52
16	2.16	10.5	6.10	3.94	8.20	41.0	114.	65.5	10.5	3.10	2.70	3.52
17	18.7	9.34	6.10	3.94	8.20	43.0	113.	58.0	10.5	2.83	2.70	3.10
18	13.8	8.58	6.70	3.31	8.20	40.0	108.	57.0	7.30	2.83	2.70	3.10
19	20.8	8.20	5.50	2.83	8.20	36.0	95.6	58.0	9.34	2.70	2.70	3.10
20	23.6	7.90	5.50	2.83	8.20	34.0	88.7	51.0	8.20	2.70	2.70	3.10
21	13.8	7.60	5.50	2.83	8.20	32.0	78.2	45.0	7.90	2.56	2.70	3.10
22	9.34	7.60	5.20	3.31	8.20	29.2	75.9	44.0	7.00	2.29	2.56	3.10
23	7.30	7.60	5.20	3.10	9.34	27.8	80.6	43.0	6.40	2.29	2.56	3.52
24	5.80	7.60	5.20	2.97	10.9	27.1	78.2	44.0	6.10	2.29	2.29	5.20
25	4.99	7.60	5.20	3.31	12.0	28.5	80.6	42.0	7.30	2.16	2.83	13.8
26	4.57	7.60	5.20	3.10	13.2	60.0	139.	41.0	7.90	2.16	3.10	11.6
27	4.36	7.90	4.57	3.10	16.8	71.3	128.	42.0	6.10	2.02	2.83	9.72
28	4.15	9.72	3.73	3.31	18.0	67.8	104.	44.0	5.20	1.75	2.56	8.96
29	7.00	10.5	3.94	3.31	-----	64.3	85.2	42.0	5.20	1.75	2.56	7.90
30	10.9	14.4	4.15	3.10	-----	58.0	71.3	32.0	8.20	1.75	2.43	7.30
31	113.	-----	4.15	2.83	-----	55.0	-----	31.3	-----	1.75	2.43	-----
Maks.	146.	126.	15.0	4.78	18.7	86.4	179.	178.	35.0	12.0	3.31	20.1
Min.	1.33	7.60	3.31	2.56	3.10	18.7	58.0	28.5	4.78	1.67	1.75	2.43
Ortalama	9.39	20.0	7.44	3.77	7.84	41.7	91.3	81.1	14.8	3.66	2.60	4.34
LT/SN/Km2	4.94	10.5	3.91	1.99	4.13	21.9	48.0	42.7	7.79	1.93	1.37	2.28
AKIM mm.	13.2	27.3	10.5	5.32	9.98	58.8	125.	114.	20.2	5.16	3.66	5.91
MİL. M3	25.2	51.9	19.9	10.1	19.0	112.	237.	217.	38.4	9.81	6.96	11.2

SU YILI (2006) YILLIK TOPLAM AKIM 758.47 MİLYON M3 399 MM. 12.6 LT/SN/Km2

22. Dogu Karadeniz Havzasi

D22A013 KAVRAZ D. SÜTTAŞI

YERİ : **TİREBOLUYA 35 KM MESAFEDEKİ DOĞUKENT BUCAĞINDADIR.**
39°54'54" Doğu - 40°47'40" Kuzey

YAĞIŞ ALANI : **125,00 km2** **YAKLAŞIK KOT : 188 m**

GÖZLEM SÜRESİ : **12.08.1967 - 30.09.2006**

ORTALAMA AKIMLAR : **Gözlem süresinde 3.022 m3/sn. (24 Yıllık) 2006 Su yılında 2.537 m3/sn.**

ANLIK EN ÇOK VE EN AZ AKIMLAR:

2006 Su yılında anlık ençok akım	**:**	**24.6**	**m3/sn**	**04.10.2005**
2006 Su yılında anlık enaz akım	**:**	**0.240**	**m3/sn**	**27.08.2006**
Gözlem süresinde anlık ençok akım	**:**	**79.0**	**m3/sn**	**30.07.1977**
Gözlem süresinde anlık enaz akım	**:**	**0.110**	**m3/sn**	**21.08.1980**

Akımlar 01 Ekim 2005 'den 30 Eylül 2006' a kadar m3/sn olarak

Gün	Ekim	Kasım	Aralık	Ocak	Şubat	Mart	Nisan	Mayıs	Haziran	Temmuz	Ağustos	Eylül
01	0.360	4.44	2.79	0.980	0.980	2.42	7.20	11.9	2.42	1.16	0.360	0.320
02	0.360	4.12	2.53	0.980	0.980	2.42	6.80	10.8	2.30	5.60	0.320	0.360
03	0.400	3.80	2.40	0.980	0.980	2.78	5.12	10.6	2.07	3.26	0.360	0.360
04	6.20	3.50	2.00	0.980	0.980	2.90	4.24	9.04	1.72	1.77	0.320	0.360
05	4.06	3.96	1.77	1.08	0.980	2.18	4.24	8.00	1.63	1.29	0.320	0.400
06	2.18	4.96	1.65	1.65	0.980	2.42	3.46	8.83	1.63	1.20	0.320	0.440
07	1.69	4.96	1.40	1.77	1.29	3.04	3.46	9.67	1.54	1.53	0.360	0.440
08	1.53	12.1	1.29	1.65	1.18	5.66	4.94	14.7	1.45	1.91	0.320	0.400
09	1.37	9.62	1.18	1.40	1.40	6.40	9.46	10.3	1.16	1.29	0.320	0.400
10	1.20	6.64	1.29	1.18	1.08	3.46	10.1	6.20	0.983	0.805	0.320	0.440
11	0.880	4.96	1.29	1.08	1.65	2.18	10.1	5.12	0.897	0.665	0.320	0.440
12	0.805	4.28	1.29	0.980	1.45	1.84	9.46	4.94	1.25	0.490	0.280	0.400
13	0.540	3.65	1.18	0.980	1.07	1.84	9.88	5.12	0.810	0.490	0.280	0.360
14	0.540	3.05	1.18	0.980	0.810	2.78	9.67	5.30	0.740	0.360	0.280	0.320
15	0.600	2.79	1.18	0.980	0.740	4.24	11.1	4.76	0.983	0.360	0.280	0.320
16	0.805	2.53	1.08	0.980	0.660	2.90	10.8	4.58	0.740	0.320	0.280	0.320
17	5.42	2.40	1.08	0.980	0.660	2.42	8.41	4.58	0.897	0.320	0.280	0.280
18	4.88	2.26	0.980	0.980	0.660	2.07	6.80	4.24	0.740	0.320	0.280	0.280
19	15.5	2.12	1.08	0.980	1.07	1.84	5.66	3.76	0.740	0.360	0.320	0.280
20	9.84	2.12	1.08	0.980	1.16	1.63	6.20	3.32	0.740	0.360	0.320	0.240
21	5.88	2.66	1.08	0.980	1.07	1.54	7.40	3.32	0.740	0.320	0.320	0.240
22	4.96	2.92	0.980	0.980	1.07	1.63	6.40	3.18	0.740	0.320	0.280	0.240
23	4.44	2.53	0.980	0.980	1.16	1.84	6.02	3.18	0.660	0.360	0.280	0.280
24	4.12	2.26	0.980	0.980	1.16	3.46	9.46	3.04	0.660	0.360	0.280	0.360
25	4.12	2.40	0.980	0.980	1.72	7.00	9.67	3.04	0.740	0.360	0.280	0.240
26	4.78	2.92	0.980	0.980	2.42	5.66	7.20	3.04	0.740	0.400	0.280	0.490
27	5.88	3.96	0.880	0.980	2.66	3.76	6.40	3.60	0.740	0.400	0.280	0.320
28	6.26	6.07	0.880	0.980	2.90	3.18	5.84	3.32	0.660	0.360	0.280	0.280
29	6.83	3.35	0.980	0.980	-----	2.90	6.40	2.78	0.740	0.400	0.320	1.91
30	5.32	3.20	0.980	0.980	-----	2.90	11.1	2.66	0.740	0.360	0.320	0.490
31	4.78	-----	0.980	0.980	-----	4.58	-----	2.66	-----	0.360	0.320	-----
Maks.	24.6	17.0	3.05	2.00	3.46	8.83	15.0	18.9	3.04	8.32	0.400	5.60
Min.	0.360	2.00	0.880	0.980	0.660	1.45	3.04	2.30	0.590	0.320	0.240	0.240
Ortalama	3.76	4.02	1.30	1.08	1.25	3.09	7.43	5.79	1.09	0.899	0.306	0.400
LT/SN/Km2	30.1	32.1	10.4	8.60	9.98	24.7	59.5	46.3	8.69	7.19	2.45	3.20
AKIM mm.	80.5	83.3	27.9	23.0	24.1	66.3	154.	124.	22.5	19.3	6.55	8.30
MİL. M3	10.1	10.4	3.49	2.88	3.02	8.28	19.3	15.5	2.82	2.41	0.819	1.04

SU YILI (2006) YILLIK TOPLAM AKIM 80.06 MİLYON M3 640 MM. 20.3 LT/SN/Km2

22. Dogu Karadeniz Havzasi

D22A040 HARSİT Ç. EYMÜR

YERİ : **TİREBOLUDAN DOĞANKENTE GİDEN YOLDA EYMÜR KÖPRÜSÜNÜN 50 M. MEMBAĞINDADIR.**
38°52'30" Doğu - 40°51'0" Kuzey

YAĞIŞ ALANI : **3133,00 km2** **YAKLAŞIK KOT : 120 m**

GÖZLEM SÜRESİ : **01.10.1976 - 30.09.2006**

ORTALAMA AKIMLAR : **Gözlem süresinde 39.660 m3/sn. (30 Yıllık) 2006 Su yılında 54.337 m3/sn.**

ANLIK EN ÇOK VE EN AZ AKIMLAR:

2006 Su yılında anlık ençok akım	**:**	**414.**	**m3/sn**	**03.05.2006**
2006 Su yılında anlık enaz akım	**:**	**2.05**	**m3/sn**	**01.10.2005**
Gözlem süresinde anlık ençok akım	**:**	**2015**	**m3/sn**	**20.06.1990**
Gözlem süresinde anlık enaz akım	**:**	**1.32**	**m3/sn**	**16.12.2003**

Akımlar 01 Ekim 2005 'den 30 Eylül 2006' a kadar m3/sn olarak

Gün	Ekim	Kasım	Aralık	Ocak	Şubat	Mart	Nisan	Mayıs	Haziran	Temmuz	Ağustos	Eylül
01	5.40	234.	40.2	15.3	10.0	50.1	123.	301.	56.5	27.4	7.32	9.60
02	4.80	113.	36.6	14.7	8.40	50.1	128.	275.	62.0	75.0	7.32	9.20
03	4.80	79.5	35.7	14.7	11.2	43.8	133.	357.	72.4	58.7	7.32	9.60
04	99.0	65.9	35.7	14.2	11.2	53.2	133.	310.	62.0	34.8	8.40	9.60
05	84.0	67.2	33.9	12.9	11.6	58.7	128.	252.	48.3	26.7	9.20	9.20
06	44.7	78.0	32.3	15.3	11.6	52.1	121.	281.	48.3	35.7	5.70	10.0
07	32.3	69.8	31.6	15.3	13.8	54.3	117.	272.	48.3	41.1	2.64	11.8
08	28.8	155.	14.7	15.3	12.9	75.0	121.	319.	48.3	46.5	3.76	9.20
09	28.8	107.	16.9	15.3	16.9	119.	133.	362.	47.4	38.4	10.9	9.20
10	28.1	71.1	19.0	14.2	19.5	121.	138.	281.	46.5	35.7	11.3	8.80
11	30.9	56.5	19.0	15.8	27.4	109.	143.	220.	40.2	20.2	8.00	8.80
12	12.4	45.6	19.0	15.3	23.4	68.5	143.	183.	41.1	11.6	9.60	12.7
13	14.7	42.0	14.2	13.8	22.1	49.2	202.	170.	33.9	4.80	9.20	11.8
14	24.7	39.3	9.20	14.2	20.2	46.5	220.	180.	30.9	9.60	9.20	8.80
15	26.7	37.5	13.8	14.2	19.5	57.6	218.	160.	19.0	9.20	9.20	7.28
16	42.0	36.6	13.8	13.3	18.4	59.8	173.	140.	29.5	3.76	9.20	6.92
17	38.4	24.1	10.0	12.0	17.9	57.6	148.	135.	30.9	8.00	8.80	6.92
18	41.1	22.8	7.32	11.6	12.9	55.4	128.	135.	30.2	8.40	9.20	7.28
19	186.	22.8	8.40	10.4	24.7	54.3	121.	130.	29.5	8.40	9.20	6.56
20	121.	22.1	14.7	10.0	32.3	48.3	125.	128.	30.2	9.20	10.4	3.76
21	82.5	22.8	14.2	10.8	24.1	43.8	125.	125.	28.8	4.54	11.8	5.84
22	63.3	26.0	15.3	10.4	22.1	44.7	123.	109.	19.5	3.76	14.0	6.92
23	49.2	25.4	16.9	10.0	30.9	44.7	270.	96.0	19.0	10.8	8.40	7.28
24	33.9	23.4	12.9	10.8	29.5	48.3	313.	59.8	18.4	9.60	9.20	9.60
25	32.3	17.4	12.4	10.4	49.2	73.7	226.	96.0	18.4	13.3	9.20	7.28
26	36.6	20.2	13.3	10.4	33.9	117.	178.	94.5	18.4	8.40	9.20	8.80
27	26.7	21.5	12.9	16.9	54.3	78.0	178.	99.0	17.9	8.40	8.80	8.80
28	55.4	25.4	12.4	14.2	52.1	90.0	153.	96.0	18.4	7.66	8.80	7.28
29	84.0	23.4	12.4	10.0	-----	67.2	140.	94.5	18.4	8.00	9.20	77.6
30	63.3	28.8	13.8	14.7	-----	54.3	231.	94.5	19.0	9.20	5.84	322.
31	109.	-----	13.8	10.4	-----	59.8	-----	93.0	-----	8.00	7.64	-----
Maks.	304.	325.	49.2	42.0	87.0	202.	383.	414.	81.0	160.	51.2	351.
Min.	2.05	6.98	3.07	4.54	5.10	20.2	87.0	16.3	3.76	2.64	2.05	2.20
Ortalama	49.5	54.1	18.6	13.1	22.9	64.7	161.	182.	35.1	19.5	8.64	21.3
LT/SN/Km2	15.8	17.3	5.93	4.19	7.32	20.6	51.4	58.2	11.2	6.23	2.76	6.79
AKIM mm.	42.3	44.8	15.9	11.2	17.7	55.3	133.	156.	29.0	16.7	7.39	17.6
MİL. M3	133.	140.	49.8	35.1	55.5	173.	418.	488.	90.9	52.3	23.2	55.2

SU YILI (2006) YILLIK TOPLAM AKIM 1714.00 MİLYON M3 547 MM. 17.3 LT/SN/Km2

22. Dogu Karadeniz Havzasi

D22A044 KARADERE AYTAS

YERİ : **TRABZON-RİZE YOLUNUN ARAKLIDAN SAĞA SAPILAN DAĞBAŞI YOLUNUN 36. KM SİNDEDİR.**
39°54'0" Doğu - 40°41'15" Kuzey

YAĞIŞ ALANI : **421,00 km2** **YAKLAŞIK KOT : 500 m**

GÖZLEM SÜRESİ : **01.10.1977 - 30.09.2006**

ORTALAMA AKIMLAR : **Gözlem süresinde 7.128 m3/sn. (11 Yıllık) 2006 Su yılında 8.606 m3/sn.**

ANLIK EN ÇOK VE EN AZ AKIMLAR:

2006 Su yılında anlık ençok akım	:	**57.5**	**m3/sn**	**31.10.2005**
2006 Su yılında anlık enaz akım	:	**0.813**	**m3/sn**	**29.01.2006**
Gözlem süresinde anlık ençok akım	:	**181.**	**m3/sn**	**08.05.1999**
Gözlem süresinde anlık enaz akım	:	**0.210**	**m3/sn**	**31.07.1980**

Akımlar 01 Ekim 2005 'den 30 Eylül 2006' a kadar m3/sn olarak

Gün	Ekim	Kasım	Aralık	Ocak	Şubat	Mart	Nisan	Mayıs	Haziran	Temmuz	Ağustos	Eylül
01	1.43	31.0	10.9	2.47	1.25	4.55	19.9	35.5	16.1	2.47	2.76	1.08
02	1.17	24.8	9.54	2.36	1.25	4.74	21.7	38.5	15.4	2.58	2.48	1.17
03	2.95	19.9	10.4	2.25	1.34	5.52	15.0	42.5	14.3	2.58	2.36	1.17
04	10.1	17.1	11.9	2.14	1.34	5.52	13.3	37.5	13.3	2.80	2.24	1.36
05	4.19	16.1	11.9	2.25	1.25	4.55	12.9	35.5	12.2	2.58	2.12	1.36
06	2.69	15.4	10.1	2.36	1.34	4.55	11.9	35.5	11.5	3.55	2.00	1.27
07	2.25	14.7	8.22	2.36	1.61	5.52	15.0	37.0	11.9	3.87	1.89	1.36
08	2.14	16.4	7.02	2.36	1.61	7.74	17.5	38.5	10.7	8.99	1.89	1.17
09	1.92	15.4	6.30	2.14	1.81	12.9	30.5	37.5	9.26	6.69	1.89	1.08
10	1.70	13.3	5.72	1.92	1.52	8.22	33.5	33.5	8.22	5.46	1.89	1.08
11	1.61	11.5	5.13	1.92	1.81	5.91	36.0	30.5	7.50	4.74	1.89	1.08
12	1.34	10.4	4.74	1.70	1.92	5.13	34.5	29.5	7.26	4.56	1.67	1.56
13	1.34	8.70	4.03	1.81	1.81	4.55	34.0	29.0	6.30	4.04	1.67	1.56
14	1.52	7.74	3.71	1.70	1.70	4.74	34.0	29.0	5.72	3.72	1.67	1.36
15	3.40	7.02	3.55	1.61	1.61	7.02	36.0	26.6	5.52	3.88	1.56	1.27
16	2.80	6.54	3.71	1.25	1.43	6.54	35.0	25.3	4.94	3.56	1.56	1.17
17	7.98	6.11	3.25	1.17	1.25	6.30	31.5	26.2	5.13	3.40	1.45	1.08
18	7.50	5.52	3.25	1.34	1.61	6.54	30.5	26.6	4.94	3.40	1.56	1.08
19	8.98	5.33	3.10	1.52	2.25	6.11	28.0	23.5	4.35	3.72	1.56	0.990
20	10.1	4.94	2.95	1.52	2.25	5.52	28.5	21.7	3.71	4.38	1.56	0.910
21	7.74	4.94	2.80	1.43	2.14	4.94	31.5	21.7	3.40	5.64	1.56	0.910
22	7.26	4.94	2.58	1.43	2.36	5.13	29.5	21.7	3.25	5.46	1.45	1.27
23	6.54	4.19	2.58	1.43	2.80	5.91	29.0	22.1	3.10	4.56	1.36	2.36
24	5.91	4.03	2.69	1.34	2.95	8.46	42.0	21.7	3.10	4.20	1.27	1.36
25	5.13	4.03	2.58	1.34	3.40	17.5	39.0	20.8	2.95	3.88	1.27	1.17
26	6.11	4.03	2.47	1.43	3.87	16.8	34.0	20.8	2.95	3.72	1.27	1.08
27	6.54	4.19	1.81	1.34	4.19	12.9	29.0	21.2	2.95	3.56	1.27	1.08
28	7.02	6.11	2.14	1.34	4.03	11.9	26.6	20.3	3.25	3.72	1.17	1.08
29	8.98	8.46	2.25	1.17	-----	11.9	25.3	17.5	2.95	3.72	1.08	0.990
30	11.9	12.6	2.14	1.17	-----	12.2	35.0	16.4	2.47	3.40	1.08	1.17
31	41.0	-----	2.36	1.25	-----	15.7	-----	16.4	-----	3.08	1.08	-----
Maks.	57.5	33.5	12.6	2.58	4.55	21.7	45.8	49.2	17.1	10.9	2.92	5.64
Min.	1.10	1.17	1.34	0.813	0.870	4.03	11.2	15.7	2.36	2.47	1.08	0.910
Ortalama	6.17	10.5	5.03	1.70	2.06	7.92	28.0	27.7	6.95	4.06	1.66	1.22
LT/SN/Km2	14.7	25.0	11.9	4.05	4.89	18.8	66.5	65.9	16.5	9.65	3.95	2.90
AKIM mm.	39.2	64.7	32.0	10.8	11.8	50.4	172.	176.	42.8	25.8	10.6	7.52
MİL. M3	16.5	27.3	13.5	4.56	4.99	21.2	72.6	74.3	18.0	10.9	4.45	3.16

SU YILI (2006) YILLIK TOPLAM AKIM 271.46 MİLYON M3 645 MM. 20.4 LT/SN/Km2

22. Dogu Karadeniz Havzasi

D22A049 KAPİSTRE D. BAŞKÖY

YERİ : **RİZE ARTVİN YOLUNDA ARHAVİ'DEN SAĞA AYRILAN ORTACALAR YOLUNUN 6.KM SİNDEKİ KONARLI BUCAĞINDAN 2 KM İLERİDEDİR.**
41°19'49" Doğu - 41°18'28" Kuzey

YAĞIŞ ALANI : **186,20 km2** **YAKLAŞIK KOT : 100 m**

GÖZLEM SÜRESİ : **01.10.1977 - 30.09.2006**

ORTALAMA AKIMLAR : **Gözlem süresinde 10.449 m3/sn. (13 Yıllık) 2006 Su yılında 10.867 m3/sn.**

ANLIK EN ÇOK VE EN AZ AKIMLAR:

2006 Su yılında anlık ençok akım	:	**318.**	**m3/sn**	**05.10.2005**
2006 Su yılında anlık enaz akım	:	**1.62**	**m3/sn**	**31.08.2006**
Gözlem süresinde anlık ençok akım	:	**440.**	**m3/sn**	**03.09.1996**
Gözlem süresinde anlık enaz akım	:	**0.790**	**m3/sn**	**23.08.1999**

Akımlar 01 Ekim 2005 'den 30 Eylül 2006' a kadar m3/sn olarak

Gün	Ekim	Kasım	Aralık	Ocak	Şubat	Mart	Nisan	Mayıs	Haziran	Temmuz	Ağustos	Eylül
01	4.16	33.5	14.4	2.62	2.34	15.3	18.1	14.4	12.1	17.1	5.22	1.68
02	2.83	20.8	13.5	4.08	2.76	19.2	14.8	17.1	12.1	23.0	4.58	1.76
03	4.16	17.1	17.5	3.76	3.60	15.7	13.5	19.2	10.8	48.9	4.16	2.94
04	59.8	13.9	11.7	3.18	4.08	19.7	9.48	16.6	9.92	25.1	3.74	7.98
05	110.	12.7	7.58	2.90	3.76	11.7	8.26	15.7	8.60	16.6	3.38	8.76
06	46.1	13.9	5.88	2.76	4.24	13.0	9.92	17.5	8.60	15.3	3.16	16.2
07	42.6	11.7	4.72	3.76	7.92	13.9	9.92	18.6	13.0	14.4	2.94	32.8
08	32.1	48.9	4.24	4.56	5.20	17.5	16.2	16.6	9.92	30.7	2.83	8.50
09	17.5	31.4	3.76	5.04	8.26	22.5	22.5	16.2	7.58	18.1	3.27	4.72
10	12.4	17.5	3.60	4.08	6.90	15.7	20.8	13.9	6.56	12.0	3.05	3.49
11	9.80	18.1	3.46	3.32	9.48	9.04	23.0	11.7	5.04	9.54	2.72	3.05
12	9.02	50.3	3.76	2.76	12.1	8.60	19.7	12.1	10.4	7.98	2.61	3.88
13	8.24	21.9	3.46	2.62	7.92	9.48	19.7	13.9	5.54	6.76	2.50	11.1
14	7.46	14.8	3.04	2.90	5.04	10.8	18.6	24.4	5.04	6.32	2.50	5.66
15	12.4	11.7	2.90	3.04	4.08	14.4	19.2	15.7	4.56	12.0	2.42	6.32
16	9.54	10.1	3.92	2.76	3.46	12.6	20.8	13.0	4.40	7.98	2.42	7.20
17	23.7	9.02	4.08	2.48	3.04	9.04	13.9	16.6	5.54	6.32	2.42	8.50
18	19.2	8.24	3.46	2.34	13.5	7.92	12.1	15.3	8.60	6.32	2.34	5.00
19	44.7	7.72	3.18	2.13	7.92	8.26	10.8	12.6	6.22	9.02	5.88	3.74
20	53.8	7.20	3.76	3.46	5.88	8.60	13.0	13.0	4.24	11.1	4.58	3.05
21	61.6	7.46	3.76	2.76	5.88	6.90	20.8	13.5	3.92	10.1	3.05	2.83
22	30.7	8.76	3.46	3.04	7.24	7.58	15.3	13.0	3.92	9.54	2.72	3.60
23	18.1	7.72	3.32	3.46	7.92	8.60	13.0	12.6	3.76	8.24	2.34	3.49
24	13.9	6.76	3.32	2.90	9.48	16.6	17.5	12.1	3.76	7.72	2.17	2.94
25	11.7	6.76	3.32	2.62	13.9	18.1	22.5	13.9	4.08	7.20	2.17	2.50
26	17.1	8.76	3.32	2.48	15.3	14.8	13.0	14.4	6.90	5.88	2.09	3.74
27	12.7	9.80	3.04	2.76	15.3	9.48	8.60	13.9	6.56	5.66	1.84	4.30
28	65.2	11.7	2.90	2.90	13.0	7.24	9.04	13.5	5.20	5.88	1.84	3.38
29	51.0	9.02	2.76	2.62	-----	8.26	9.48	8.60	6.22	10.4	1.76	2.72
30	25.8	26.5	2.62	2.34	-----	9.48	17.1	9.92	4.88	8.76	1.76	2.72
31	25.1	-----	2.62	2.20	-----	11.2	-----	11.7	-----	6.32	1.68	-----
Maks.	318.	85.0	24.4	39.1	20.8	37.7	33.5	30.7	19.2	113.	41.9	146.
Min.	2.50	6.10	2.48	2.13	2.20	6.22	7.24	6.56	3.32	5.22	1.62	1.62
Ortalama	27.8	16.1	5.04	3.05	7.48	12.3	15.4	14.6	6.93	12.6	2.91	5.95
LT/SN/Km2	149.	86.6	27.1	16.4	40.2	66.0	82.5	78.2	37.2	67.6	15.6	32.0
AKIM mm.	400.	224.	72.5	43.9	97.2	177.	214.	209.	96.5	181.	41.8	82.9
MİL. M3	74.5	41.8	13.5	8.18	18.1	32.9	39.8	39.0	18.0	33.7	7.79	15.4

SU YILI (2006) YILLIK TOPLAM AKIM 342.67 MİLYON M3 1840 MM. 58.4 LT/SN/Km2

22. Dogu Karadeniz Havzasi

D22A052 SOLAKLI D. ULUCAMİ

YERİ : **TRABZON - RİZE YOLUNUN DERNEK PAZARINDAN 4 KM SONRA ULUCAMİİ KÖPRÜSÜNDEDİR. 40°15'20" Doğu - 40°46'0" Kuzey**

YAĞIŞ ALANI : **577,00 km2** **YAKLAŞIK KOT : 275 m**

GÖZLEM SÜRESİ : **10.08.1978 - 30.09.2006**

ORTALAMA AKIMLAR : **Gözlem süresinde 14.594 m3/sn. (27 Yıllık) 2006 Su yılında 15.546 m3/sn.**

ANLIK EN ÇOK VE EN AZ AKIMLAR:

2006 Su yılında anlık ençok akım	:	**62.8**	**m3/sn**	**09.05.2006**
2006 Su yılında anlık enaz akım	:	**3.05**	**m3/sn**	**01.10.2005**
Gözlem süresinde anlık ençok akım	:	**177.**	**m3/sn**	**03.08.2005**
Gözlem süresinde anlık enaz akım	:	**2.20**	**m3/sn**	**16.10.1979**

Akımlar 01 Ekim 2005 'den 30 Eylül 2006' a kadar m3/sn olarak

Gün	Ekim	Kasım	Aralık	Ocak	Şubat	Mart	Nisan	Mayıs	Haziran	Temmuz	Ağustos	Eylül
01	3.33	38.9	19.7	6.22	5.32	9.80	16.5	41.1	30.5	12.9	11.3	6.46
02	3.92	28.5	16.5	6.70	5.32	9.80	18.1	36.7	31.5	13.7	10.7	6.46
03	4.78	26.0	14.1	6.46	5.32	10.4	21.4	43.3	30.5	14.5	10.4	6.46
04	6.70	26.0	15.3	6.46	5.32	11.0	21.9	53.2	29.5	15.3	9.80	7.54
05	15.7	25.5	15.7	6.22	5.50	12.9	22.3	50.8	29.0	14.1	9.50	7.54
06	10.4	26.0	14.9	6.22	5.32	10.4	20.5	45.5	27.5	15.7	9.22	6.98
07	9.80	28.0	13.3	6.70	5.50	9.80	18.5	44.4	27.5	17.3	8.94	6.98
08	11.0	24.1	11.9	6.70	7.54	9.80	18.9	51.4	28.5	25.0	8.66	6.70
09	10.7	38.9	11.0	7.54	6.70	12.5	20.1	55.6	26.5	19.7	8.94	6.46
10	10.4	32.0	10.4	7.82	7.82	26.0	27.0	50.2	23.2	16.5	8.94	6.46
11	9.80	23.7	10.1	7.26	7.26	18.5	34.0	43.3	21.9	15.3	8.38	6.46
12	9.50	19.7	9.50	6.70	6.98	13.7	40.5	38.9	20.5	14.1	8.10	7.26
13	8.94	17.3	9.22	6.22	7.26	12.5	40.5	38.3	21.0	13.3	8.10	7.82
14	8.66	16.1	8.38	5.98	6.98	11.9	41.6	39.4	18.5	12.5	7.82	7.26
15	8.38	14.9	8.10	6.46	6.70	11.6	44.4	39.4	18.9	12.9	7.82	7.54
16	10.7	13.7	7.82	5.74	6.70	13.7	44.9	34.0	18.5	11.9	7.82	6.98
17	9.80	12.9	7.82	5.98	6.22	12.9	34.5	32.5	17.3	11.6	7.82	6.70
18	21.0	11.9	7.54	5.74	5.74	12.2	31.5	35.0	18.5	11.6	7.26	6.46
19	20.5	11.3	6.98	5.74	5.98	11.9	29.0	35.6	17.7	12.9	7.54	5.98
20	21.0	10.7	6.98	5.74	9.50	11.6	30.5	31.5	16.1	14.5	7.82	5.98
21	20.1	10.4	7.26	4.96	8.66	11.6	35.6	30.0	15.3	15.3	7.26	5.98
22	16.9	11.0	7.26	5.98	7.82	11.0	35.0	31.5	14.1	14.9	7.26	6.46
23	16.1	11.3	6.98	5.74	7.82	10.4	34.5	32.5	14.1	13.3	6.98	6.98
24	15.7	10.4	6.98	5.98	7.82	10.4	43.3	32.5	14.1	12.9	6.98	6.22
25	15.3	9.50	7.26	5.74	8.10	12.2	43.3	32.0	13.7	12.9	6.98	5.98
26	14.9	9.50	7.26	5.50	8.66	18.9	34.0	33.5	13.7	12.2	6.98	6.46
27	15.7	9.80	7.26	5.50	9.80	19.3	28.5	34.5	13.7	11.6	6.70	6.46
28	16.1	10.4	6.46	5.50	10.4	15.3	26.0	36.1	14.1	12.2	6.70	6.22
29	17.7	12.2	6.22	5.50	-----	15.3	25.0	34.5	13.3	12.9	6.46	5.98
30	17.7	14.9	6.46	5.50	-----	15.3	41.1	28.5	12.9	12.9	6.46	6.70
31	24.1	-----	6.22	5.14	-----	15.3	-----	28.0	-----	11.9	6.46	-----
Maks.	27.5	48.4	22.3	7.82	11.3	29.0	49.6	62.8	35.0	32.0	11.6	8.66
Min.	3.05	9.22	6.22	4.96	5.32	9.80	16.5	26.0	12.9	11.0	6.46	5.98
Ortalama	13.1	18.5	9.71	6.12	7.07	13.2	30.8	38.5	20.4	14.1	8.07	6.66
LT/SN/Km2	22.7	32.1	16.8	10.6	12.3	22.8	53.3	66.7	35.4	24.5	14.0	11.5
AKIM mm.	60.7	83.2	45.1	28.4	29.7	61.1	138.	179.	91.7	65.6	37.4	29.9
MİL. M3	35.0	48.0	26.0	16.4	17.1	35.2	79.7	103.	52.9	37.9	21.6	17.3

SU YILI (2006) YILLIK TOPLAM AKIM 490.10 MİLYON M3 849 MM. 26.9 LT/SN/Km2

22. Dogu Karadeniz Havzasi

D22A053 SÜRMENE D. ORTAKÖY

YERİ : **TRABZON - RİZE YOLUNUN SÜRMENE ÇIKIŞINDADIR.**
40°7'0" Doğu - 40°51'0" Kuzey

YAĞIŞ ALANI : **174,00 km2** **YAKLAŞIK KOT : 150 m**

GÖZLEM SÜRESİ : **01.10.1978 - 30.09.2006**

ORTALAMA AKIMLAR : **Gözlem süresinde 5.440 m3/sn. (17 Yıllık) 2006 Su yılında 6.071 m3/sn.**

ANLIK EN ÇOK VE EN AZ AKIMLAR:

2006 Su yılında anlık ençok akım	**:**	**119.**	**m3/sn**	**03.07.2006**
2006 Su yılında anlık enaz akım	**:**	**0.968**	**m3/sn**	**21.11.2005**
Gözlem süresinde anlık ençok akım	**:**	**217.**	**m3/sn**	**02.08.2005**
Gözlem süresinde anlık enaz akım	**:**	**0.260**	**m3/sn**	**24.01.1984**

Akımlar 01 Ekim 2005 'den 30 Eylül 2006' a kadar m3/sn olarak

Gün	Ekim	Kasım	Aralık	Ocak	Şubat	Mart	Nisan	Mayıs	Haziran	Temmuz	Ağustos	Eylül
01	1.10	30.5	6.84	3.80	2.84	6.20	6.20	20.7	3.64	3.16	5.72	2.68
02	1.10	20.0	5.48	5.72	2.84	6.84	7.80	17.3	3.48	10.4	5.24	2.68
03	3.48	5.72	4.04	4.52	2.84	6.52	9.08	19.5	3.16	38.5	5.00	2.84
04	15.6	4.04	4.04	3.80	2.84	6.84	14.0	22.1	2.68	29.8	4.76	4.04
05	5.48	3.00	3.80	3.48	4.04	8.44	11.4	20.0	2.68	15.6	4.52	4.76
06	3.00	3.80	4.28	3.32	4.04	6.52	8.44	16.2	2.52	15.6	4.28	3.64
07	1.92	4.28	4.04	3.64	4.76	5.96	7.80	14.0	2.36	17.8	4.04	5.24
08	1.92	3.48	3.80	4.04	8.76	5.72	7.48	12.5	2.20	17.8	3.80	6.84
09	1.64	22.8	3.64	9.40	6.20	8.76	8.76	12.5	2.06	22.8	3.80	4.04
10	1.50	3.48	3.64	6.84	7.80	14.0	15.6	11.4	1.78	15.1	3.64	3.48
11	1.50	2.06	3.64	5.00	5.96	9.40	15.1	9.40	1.50	9.91	3.48	3.16
12	1.50	1.64	3.48	3.80	9.08	7.48	15.1	7.80	3.16	8.12	3.32	3.16
13	1.42	1.34	3.64	3.32	7.80	6.52	15.1	7.48	5.24	7.16	3.16	6.52
14	1.42	1.34	3.64	3.32	5.72	5.48	14.5	7.80	2.84	6.84	3.16	5.48
15	1.42	1.10	3.64	3.48	4.76	5.72	15.1	15.6	1.92	6.52	3.16	4.52
16	3.64	1.03	3.32	3.64	4.04	6.52	15.1	8.44	2.36	7.16	3.16	3.80
17	3.48	1.26	3.16	3.48	3.64	5.72	14.5	8.12	2.36	5.96	3.16	3.48
18	9.40	1.18	3.00	3.32	3.48	5.24	10.4	7.80	8.76	5.24	3.00	3.32
19	8.12	1.03	2.84	3.16	3.80	5.00	9.08	6.84	6.20	5.48	3.00	3.16
20	22.1	1.03	2.68	3.00	9.91	5.48	7.80	5.96	4.04	6.52	3.16	3.00
21	17.8	0.968	3.64	3.16	7.16	5.72	8.12	5.48	3.00	8.44	3.00	2.84
22	5.48	1.03	3.80	3.16	5.72	5.00	9.08	5.24	2.52	9.40	2.84	2.84
23	3.80	1.34	3.48	3.16	5.48	4.76	8.76	5.00	2.20	7.80	2.84	4.04
24	3.48	1.26	3.48	3.32	5.48	4.76	9.91	4.76	1.92	6.84	2.68	4.28
25	3.32	1.26	4.04	3.00	5.24	6.52	25.6	4.52	1.78	5.96	2.68	3.48
26	3.00	1.18	4.52	3.00	7.16	9.08	30.5	4.28	1.78	5.48	2.68	3.16
27	3.64	1.26	4.04	2.84	8.76	8.76	18.9	5.72	1.92	5.24	2.68	8.12
28	3.80	1.42	3.48	3.00	8.12	6.52	13.0	6.20	2.06	5.24	2.68	5.48
29	5.00	2.36	3.64	3.00	-----	5.96	10.9	4.76	3.00	5.48	2.68	4.04
30	10.9	2.68	3.80	3.00	-----	5.72	10.4	4.04	3.80	5.48	2.68	3.64
31	12.0	-----	3.80	2.84	-----	5.48	-----	3.64	-----	6.52	2.68	-----
Maks.	113.	66.7	6.84	12.5	16.2	15.6	41.2	31.9	10.4	119.	5.96	21.4
Min.	1.03	0.968	2.52	2.84	2.68	3.64	6.20	3.48	1.42	3.16	2.52	2.52
Ortalama	5.26	4.30	3.82	3.79	5.65	6.67	12.5	9.84	2.96	10.6	3.44	4.06
LT/SN/Km2	30.2	24.7	21.9	21.8	32.5	38.3	71.6	56.6	17.0	60.7	19.8	23.3
AKIM mm.	80.9	64.0	58.8	58.4	78.6	103.	185.	151.	44.2	163.	53.0	60.5
MİL. M3	14.1	11.1	10.2	10.2	13.7	17.9	32.3	26.4	7.68	28.3	9.22	10.5

SU YILI (2006) YILLIK TOPLAM AKIM 191.60 MİLYON M3 1101 MM. 34.9 LT/SN/Km2

22. Dogu Karadeniz Havzasi

D22A058 GÖRELE D. CÜCEN KÖPRÜ

YERİ : **ÇANAKCIDAN 6 KM YUKARIDADIR.**
39°0'40" Doğu - 40°53'6" Kuzey

YAĞIŞ ALANI : **163,00 km2** **YAKLAŞIK KOT : 300 m**

GÖZLEM SÜRESİ : **08.06.1979 - 30.09.2006**

ORTALAMA AKIMLAR : **Gözlem süresinde 4.725 m3/sn. (24 Yıllık) 2006 Su yılında 4.725 m3/sn.**

ANLIK EN ÇOK VE EN AZ AKIMLAR:

2006 Su yılında anlık ençok akım	**:**	**83.8**	**m3/sn**	**03.07.2006**
2006 Su yılında anlık enaz akım	**:**	**0.600**	**m3/sn**	**08.12.2005**
Gözlem süresinde anlık ençok akım	**:**	**202.**	**m3/sn**	**14.10.1988**
Gözlem süresinde anlık enaz akım	**:**	**0.220**	**m3/sn**	**05.10.1999**

5. Anahtar Eğrisi (Seviyeler cm olarak)

Seviye	Akım	Seviye	Akım	Seviye	Akım	Seviye	Akım
60	0.170	95	1.7	160	17.6	250	47.4
64	0.220	110	3.6	170	20.8	300	64.4
68	0.290	130	8.4	180	24.0	350	81.4
75	0.450	140	11.2	190	27.2	400	100.
85	0.920	150	14.4	200	30.4	500	140.

Akımlar 01 Ekim 2005 'den 30 Eylül 2006' a kadar m3/sn olarak

Gün	Ekim	Kasım	Aralık	Ocak	Şubat	Mart	Nisan	Mayıs	Haziran	Temmuz	Ağustos	Eylül
01	13.3	14.0	12.8	1.91	1.73	9.00	5.81	8.00	1.39	6.15	2.00	1.39
02	13.3	12.8	2.72	2.72	1.73	10.3	8.20	5.47	1.55	34.9	1.73	1.39
03	13.3	6.66	1.91	2.48	1.73	10.3	9.00	5.81	1.73	45.1	1.55	1.09
04	28.0	5.47	1.91	2.12	1.73	11.0	13.5	7.40	1.82	27.1	1.39	1.23
05	37.0	4.40	1.39	2.00	1.55	11.0	12.1	5.15	1.91	13.3	1.23	1.39
06	37.0	10.3	1.03	2.12	1.55	8.00	9.22	4.10	2.12	8.20	1.15	1.09
07	17.8	16.9	0.792	6.83	1.64	8.80	6.83	5.47	2.12	9.00	1.03	3.08
08	6.32	11.0	0.696	4.40	3.80	9.44	6.66	5.30	2.00	17.2	0.964	3.68
09	4.70	39.4	0.792	3.80	2.84	15.3	9.44	16.6	2.00	16.3	0.964	1.73
10	3.56	20.8	0.902	2.84	4.55	15.5	11.2	8.80	1.91	7.80	0.964	1.23
11	2.24	8.00	0.902	2.00	2.96	7.40	9.44	4.70	2.00	4.85	0.964	1.09
12	1.82	4.40	0.902	1.64	5.81	5.30	9.00	2.72	1.91	3.68	0.964	1.03
13	1.64	7.60	0.840	1.39	5.47	4.85	8.20	1.73	1.39	3.20	1.03	5.81
14	1.47	5.15	1.03	1.39	3.44	4.70	7.60	1.47	0.964	2.84	1.09	3.80
15	1.31	3.32	1.09	1.39	2.48	6.83	6.15	3.32	1.47	2.24	1.09	2.36
16	1.47	2.36	1.15	1.39	2.00	10.3	5.81	2.24	0.840	1.91	1.09	1.91
17	2.00	1.73	1.15	1.47	1.55	6.66	5.98	1.55	1.23	1.73	1.09	1.55
18	3.56	1.31	1.15	1.55	1.64	5.00	4.10	1.47	1.23	1.73	1.09	1.31
19	1.91	1.03	1.31	1.55	2.00	3.95	3.44	1.39	0.964	2.60	1.09	1.15
20	23.8	0.840	1.39	1.64	9.44	3.80	2.96	1.09	1.03	3.08	1.09	1.03
21	42.7	0.792	1.15	1.39	6.66	3.68	2.96	0.902	1.31	3.20	2.12	1.03
22	17.2	1.03	1.03	1.39	5.15	3.68	3.20	0.744	1.47	2.84	1.91	1.03
23	12.6	1.82	1.15	1.47	5.81	4.40	2.84	0.792	1.64	2.48	1.03	1.09
24	5.15	1.31	1.09	1.39	6.15	5.47	2.84	0.902	1.64	2.48	1.09	1.91
25	3.56	1.15	0.964	1.47	7.40	10.1	6.49	1.03	1.64	2.36	1.15	3.68
26	2.36	1.55	0.902	1.47	8.80	9.22	19.9	1.09	1.73	2.24	1.15	1.55
27	1.91	2.84	1.23	1.47	12.8	6.66	9.88	1.23	1.31	2.00	1.15	3.44
28	6.49	2.60	1.31	1.55	12.4	4.40	7.20	1.64	1.31	2.00	1.23	3.08
29	2.84	2.72	1.55	1.64	-----	4.10	6.32	0.964	1.23	2.36	1.31	1.91
30	18.7	2.12	1.64	1.73	-----	4.25	6.66	0.840	1.31	2.72	1.31	1.64
31	22.9	-----	1.91	1.73	-----	4.40	-----	1.15	-----	2.72	1.39	-----
Maks.	75.2	49.3	12.8	6.83	19.0	25.6	28.3	30.4	2.96	83.8	17.2	17.8
Min.	1.15	0.792	0.600	1.31	1.31	3.32	2.60	0.696	0.696	1.64	0.902	0.964
Ortalama	11.4	6.51	1.61	2.04	4.46	7.35	7.43	3.39	1.54	7.75	1.24	1.96
LT/SN/Km2	69.6	40.0	9.85	12.5	27.3	45.1	45.6	20.8	9.44	47.6	7.60	12.0
AKIM mm.	187.	104.	26.4	33.6	66.2	121.	118.	55.7	24.5	127.	20.4	31.1
MİL. M3	30.4	16.9	4.30	5.47	10.8	19.7	19.3	9.08	3.99	20.8	3.32	5.07

SU YILI (2006) YILLIK TOPLAM AKIM 149.13 MİLYON M3 915 MM. 29.0 LT/SN/Km2

22. Dogu Karadeniz Havzasi

D22A059 KALYON D. ÇİFTDERE

YERİ : **TRABZON MAÇKA YOLUNUN 17. KM SİNDEKİ ÇİFTDERE KÖYÜNDEDİR.**
39°41'55" Doğu - 40°51'0" Kuzey

YAĞIŞ ALANI : **122,00 km2** **YAKLAŞIK KOT : 250 m**

GÖZLEM SÜRESİ : **04.07.1979 - 31.05.2006**

ORTALAMA AKIMLAR : **Gözlem süresinde 2.667 m3/sn. (25 Yıllık) 2006 Su yılında ---- m3/sn.**

ANLIK EN ÇOK VE EN AZ AKIMLAR:

2006 Su yılında anlık ençok akım	:	**----- m3/sn**	
2006 Su yılında anlık enaz akım	:	**----- m3/sn**	
Gözlem süresinde anlık ençok akım	:	**135. m3/sn**	**20.06.1990**
Gözlem süresinde anlık enaz akım	:	**0.229 m3/sn**	**01.09.1997**

Akımlar 01 Ekim 2005 'den 30 Eylül 2006' a kadar m3/sn olarak

Gün	Ekim	Kasım	Aralık	Ocak	Şubat	Mart	Nisan	Mayıs	Haziran	Temmuz	Ağustos	Eylül
01	0.842	19.5	5.06	2.42	1.30	4.06	3.72	9.21	-----	-----	-----	-----
02	0.842	10.2	4.40	2.42	1.22	3.89	4.84	8.92	-----	-----	-----	-----
03	1.22	7.76	4.23	2.28	1.44	3.38	5.28	11.6	-----	-----	-----	-----
04	4.06	7.47	4.06	2.14	1.58	2.87	5.28	8.92	-----	-----	-----	-----
05	5.50	6.89	3.89	2.28	1.86	2.42	5.06	7.76	-----	-----	-----	-----
06	4.84	6.60	3.55	2.28	1.72	2.00	5.06	5.72	-----	-----	-----	-----
07	4.62	6.38	2.87	2.14	1.86	2.42	5.06	5.06	-----	-----	-----	-----
08	4.23	5.94	2.70	2.14	2.42	3.55	5.72	5.94	-----	-----	-----	-----
09	3.38	5.72	2.56	2.00	2.87	5.50	7.18	7.47	-----	-----	-----	-----
10	2.42	4.62	2.42	2.00	3.38	4.84	8.05	6.60	-----	-----	-----	-----
11	1.58	3.89	2.28	1.86	3.55	4.40	7.76	6.38	-----	-----	-----	-----
12	1.15	3.89	2.14	1.86	3.55	3.89	7.76	6.16	-----	-----	-----	-----
13	0.920	3.38	1.86	1.72	3.55	3.55	8.63	6.16	-----	-----	-----	-----
14	1.07	3.04	1.86	1.58	3.55	3.38	9.21	7.76	-----	-----	-----	-----
15	1.15	3.04	2.00	1.44	3.38	3.55	8.92	8.92	-----	-----	-----	-----
16	1.30	3.04	1.86	1.30	2.87	3.72	8.63	6.60	-----	-----	-----	-----
17	6.38	2.87	1.86	1.22	3.21	3.55	8.05	6.16	-----	-----	-----	-----
18	8.34	2.56	1.86	1.15	3.38	3.38	6.38	5.94	-----	-----	-----	-----
19	9.50	2.28	1.86	1.15	3.55	3.04	5.72	5.50	-----	-----	-----	-----
20	7.18	2.28	1.72	1.07	3.89	2.87	5.94	5.06	-----	-----	-----	-----
21	5.94	2.28	1.58	1.15	3.89	2.70	6.38	4.62	-----	-----	-----	-----
22	4.84	2.56	1.58	1.22	3.72	2.56	8.63	4.23	-----	-----	-----	-----
23	4.06	2.42	1.58	1.30	3.55	2.42	12.7	4.06	-----	-----	-----	-----
24	3.72	2.14	1.58	1.30	3.38	2.28	18.0	4.06	-----	-----	-----	-----
25	3.55	2.14	1.72	1.30	3.72	2.70	17.0	4.06	-----	-----	-----	-----
26	3.72	3.21	1.72	1.22	4.40	3.38	8.92	4.06	-----	-----	-----	-----
27	4.06	3.72	1.58	1.15	5.28	4.06	6.89	4.06	-----	-----	-----	-----
28	5.72	3.89	1.72	1.22	5.28	3.89	5.50	4.06	-----	-----	-----	-----
29	12.0	5.06	1.58	1.30	-----	3.38	5.72	3.89	-----	-----	-----	-----
30	21.5	5.50	2.00	1.30	-----	3.04	6.38	3.72	-----	-----	-----	-----
31	34.0	-----	2.14	1.22	-----	2.87	-----	3.55	-----	-----	-----	-----
Maks.	37.6	24.5	5.50	2.42	5.50	5.72	21.0	13.4	--	--	--	--
Min.	0.842	2.14	1.44	1.07	1.22	1.86	3.38	3.38	--	--	--	--
Ortalama	5.60	4.81	2.38	1.62	3.12	3.34	7.61	6.01	--	--	--	--
LT/SN/Km2	45.9	39.4	19.5	13.3	25.6	27.4	62.4	49.2	--	--	--	--
AKIM mm.	123.	102.	52.3	35.5	61.9	73.3	162.	132.	--	--	--	--
MİL. M3	15.0	12.5	6.38	4.33	7.55	8.95	19.7	16.1	--	--	--	--

SU YILI (2006)

22. Dogu Karadeniz Havzasi

D22A062 HEMŞİN D. KONAKLAR

YERİ : **RİZENİN ÇAMLIHEMŞİN İLÇESİNDEN 1 KM YUKARIDA KONAKLAR KÖYÜNDEDİR.**
41°0'30" Doğu - 41°2'0" Kuzey

YAĞIŞ ALANI : **497,00 km2** **YAKLAŞIK KOT : 300 m**

GÖZLEM SÜRESİ : **01.10.1979 - 30.09.2006**

ORTALAMA AKIMLAR : **Gözlem süresinde 17.877 m3/sn. (25 Yıllık) 2006 Su yılında 23.895 m3/sn.**

ANLIK EN ÇOK VE EN AZ AKIMLAR:

2006 Su yılında anlık ençok akım	:	**135.**	**m3/sn**	**04.10.2005**
2006 Su yılında anlık enaz akım	:	**7.55**	**m3/sn**	**25.02.2006**
Gözlem süresinde anlık ençok akım	:	**193.**	**m3/sn**	**21.06.2002**
Gözlem süresinde anlık enaz akım	:	**2.10**	**m3/sn**	**02.03.1984**

Akımlar 01 Ekim 2005 'den 30 Eylül 2006' a kadar m3/sn olarak

Gün	Ekim	Kasım	Aralık	Ocak	Şubat	Mart	Nisan	Mayıs	Haziran	Temmuz	Ağustos	Eylül
01	24.0	34.4	18.1	13.7	11.5	16.8	19.8	36.6	64.0	50.9	18.3	9.84
02	20.7	28.5	18.5	13.3	11.5	18.5	19.4	42.1	64.0	53.7	17.0	9.84
03	20.7	25.0	22.6	13.3	11.5	17.3	18.5	43.2	61.1	53.0	15.6	11.3
04	79.8	22.6	20.2	13.0	11.9	17.7	17.3	38.8	60.6	48.8	14.7	13.4
05	35.0	22.6	18.5	13.0	12.2	16.4	16.8	37.7	58.3	45.2	14.3	12.9
06	24.5	25.0	17.7	14.9	12.2	16.8	16.8	40.5	60.6	38.6	13.4	21.0
07	22.1	22.6	16.8	14.1	13.3	17.3	17.3	45.4	72.3	40.4	12.9	21.9
08	19.8	43.8	16.4	14.1	13.3	19.8	21.2	47.1	57.7	39.2	12.5	14.3
09	18.1	37.7	16.0	13.7	14.5	21.6	29.0	44.9	52.0	30.0	12.9	12.0
10	16.8	27.5	16.0	13.0	14.1	17.7	30.0	40.5	48.2	26.0	12.5	11.3
11	18.9	23.6	15.6	13.0	14.9	16.0	33.3	38.3	45.4	23.7	12.0	10.9
12	14.5	31.7	15.6	12.6	16.0	16.0	33.9	41.6	47.1	22.4	12.5	13.4
13	14.1	24.5	15.2	12.6	14.5	15.6	34.4	46.0	41.6	21.0	12.0	14.7
14	13.7	21.2	14.9	12.6	13.3	16.0	35.0	47.1	43.2	20.6	12.5	12.5
15	18.5	19.4	14.9	12.2	13.0	16.8	40.5	39.4	42.7	24.6	12.5	17.4
16	16.4	18.5	15.2	11.9	12.6	16.0	42.7	38.8	39.9	21.0	12.0	19.2
17	42.7	18.1	14.9	11.9	11.5	15.6	35.5	47.6	39.4	19.2	11.6	15.6
18	34.4	17.7	14.1	11.5	11.9	15.6	33.9	47.6	38.3	19.7	12.5	12.9
19	48.7	17.3	14.1	11.5	15.2	15.2	32.2	43.8	35.5	24.2	13.4	11.6
20	52.6	17.3	14.5	12.2	14.9	14.9	35.5	46.5	34.4	24.6	12.5	10.9
21	37.7	17.3	14.1	11.2	13.7	14.5	37.7	52.0	35.0	22.8	12.9	10.6
22	31.1	17.3	13.7	13.0	13.7	14.5	35.5	56.6	33.9	21.5	12.0	12.0
23	26.0	16.8	13.7	12.6	14.1	14.9	35.0	55.4	32.8	20.1	11.3	11.6
24	24.0	16.4	13.7	11.9	14.9	17.7	41.6	56.0	32.8	19.2	10.9	12.0
25	22.6	16.4	14.1	11.9	12.6	18.5	41.0	61.7	31.1	18.8	10.9	10.9
26	26.0	17.3	13.7	11.9	13.0	18.1	31.1	65.1	32.2	17.4	10.9	18.3
27	23.6	18.1	13.0	11.9	16.8	16.8	25.5	66.3	30.6	17.4	10.6	18.8
28	34.4	19.4	13.0	11.5	16.0	16.4	24.0	61.7	32.2	18.8	10.6	16.1
29	38.3	18.5	13.3	11.5	-----	16.8	23.1	48.2	32.8	27.3	10.2	14.3
30	30.0	20.7	13.3	11.5	-----	16.8	39.4	50.4	32.8	26.0	10.2	15.6
31	32.2	-----	13.3	11.5	-----	17.3	-----	59.4	-----	20.1	9.84	-----
Maks.	135.	59.4	25.0	16.0	16.8	25.5	52.0	79.8	86.7	84.9	19.2	53.0
Min.	13.0	15.6	11.9	9.86	7.55	13.7	15.6	30.6	27.5	17.0	9.84	9.48
Ortalama	28.4	22.6	15.4	12.5	13.5	16.8	29.9	47.9	44.4	28.3	12.5	13.9
LT/SN/Km2	57.2	45.4	31.1	25.2	27.2	33.7	60.2	96.5	89.4	56.9	25.2	28.0
AKIM mm.	153.	118.	83.2	67.5	65.8	90.4	156.	258.	232.	152.	67.4	72.5
MİL. M3	76.2	58.5	41.4	33.6	32.7	44.9	77.5	128.	115.	75.7	33.5	36.0

SU YILI (2006) YILLIK TOPLAM AKIM 753.00 MİLYON M3 1515 MM. 48.1 LT/SN/Km2

22. Dogu Karadeniz Havzasi

D22A063 HALA D. MİKRON KÖP.

YERİ : **RİZE - ARTVİN YOLUNDA ÇAMLIHEMŞİN YOLU AYDER ILICALARINDADIR.**
41°1'45" Doğu - 41°2'45" Kuzey

YAĞIŞ ALANI : **239,00 km2** **YAKLAŞIK KOT : 325 m**

GÖZLEM SÜRESİ : **01.10.1979 - 30.09.2006**

ORTALAMA AKIMLAR : **Gözlem süresinde 11.691 m3/sn. (23 Yıllık) 2006 Su yılında 12.880 m3/sn.**

ANLIK EN ÇOK VE EN AZ AKIMLAR:

2006 Su yılında anlık ençok akım	:	**117.**	**m3/sn**	**04.10.2005**
2006 Su yılında anlık enaz akım	:	**2.81**	**m3/sn**	**21.01.2006**
Gözlem süresinde anlık ençok akım	:	**337.**	**m3/sn**	**14.10.1994**
Gözlem süresinde anlık enaz akım	:	**1.78**	**m3/sn**	**21.02.2001**

Akımlar 01 Ekim 2005 'den 30 Eylül 2006' a kadar m3/sn olarak

Gün	Ekim	Kasım	Aralık	Ocak	Şubat	Mart	Nisan	Mayıs	Haziran	Temmuz	Ağustos	Eylül
01	14.2	19.0	7.60	4.36	3.92	7.60	16.6	23.8	32.2	20.2	5.40	16.6
02	10.6	13.0	10.0	4.36	3.92	10.6	13.6	28.0	32.8	13.6	5.40	12.4
03	13.0	11.2	15.4	4.10	3.92	8.56	11.8	26.8	32.8	12.4	5.40	8.08
04	64.6	9.04	11.8	4.10	3.92	9.04	9.04	25.0	31.0	12.4	5.14	9.04
05	23.8	10.6	9.52	4.36	3.92	7.16	9.04	25.0	30.4	12.4	5.14	16.6
06	17.2	13.6	8.56	5.40	3.92	8.56	9.52	29.2	29.8	12.4	5.14	25.0
07	18.4	10.6	7.60	4.88	4.36	9.04	10.0	31.6	35.2	12.4	5.14	21.4
08	14.8	32.2	6.72	4.62	4.36	14.8	17.2	29.8	29.2	12.4	5.40	20.8
09	10.6	23.2	6.28	4.62	4.62	16.0	22.0	29.2	25.0	12.4	7.60	13.6
10	9.52	16.0	5.84	4.36	4.36	9.04	23.2	26.8	23.2	12.4	8.08	12.4
11	28.6	13.0	5.84	4.36	5.14	7.16	25.6	26.2	20.8	12.4	5.84	11.8
12	7.60	19.6	5.84	4.36	5.40	7.16	24.4	28.0	25.6	12.4	26.2	17.2
13	7.16	13.6	5.14	4.10	4.62	6.72	25.0	29.2	18.4	11.8	7.60	19.6
14	7.16	10.6	4.88	4.10	4.10	7.60	24.4	31.0	19.0	8.08	5.40	15.4
15	12.4	8.56	4.88	4.10	3.92	9.52	26.2	25.6	17.8	8.08	4.62	21.4
16	8.56	7.60	5.40	3.92	3.92	8.56	25.6	26.2	16.6	7.60	4.88	23.8
17	23.2	7.16	4.88	3.92	3.74	7.16	20.8	31.0	17.2	7.16	4.88	17.8
18	11.2	6.72	4.62	3.92	3.92	6.72	19.6	28.6	16.0	6.72	11.8	15.4
19	25.6	6.72	4.62	3.92	6.28	6.72	19.0	26.8	14.8	6.72	6.28	13.6
20	28.0	6.28	4.62	3.92	4.88	6.28	22.6	28.0	14.2	6.72	13.0	11.8
21	21.4	6.72	4.62	3.38	4.36	6.28	26.8	29.8	14.8	6.72	13.0	11.8
22	14.8	6.72	4.36	4.62	4.36	6.28	24.4	31.6	15.4	6.28	8.56	13.0
23	11.2	6.28	4.36	4.10	4.88	6.28	23.8	30.4	14.8	5.84	6.28	11.2
24	9.04	5.84	4.36	4.10	4.62	12.4	29.2	31.0	15.4	7.60	5.14	11.2
25	8.08	5.84	4.36	3.92	5.84	12.4	26.8	34.0	14.8	6.72	4.62	10.0
26	16.0	8.56	4.36	3.92	7.16	10.6	19.6	36.4	15.4	8.08	4.62	23.8
27	9.52	9.04	4.10	3.92	6.72	8.08	16.0	37.0	14.8	7.60	4.62	20.2
28	23.8	11.2	4.10	3.92	6.28	7.60	15.4	33.4	16.0	6.28	5.14	16.6
29	23.8	8.56	4.36	3.92	-----	8.08	14.8	28.0	14.8	5.84	4.62	14.2
30	15.4	13.0	4.36	3.92	-----	8.56	28.0	28.0	13.6	5.84	4.62	14.2
31	17.2	-----	4.36	3.92	-----	10.6	-----	31.6	-----	5.40	3.92	-----
Maks.	117.	49.6	17.2	6.28	9.52	22.6	36.4	46.6	40.6	38.2	68.8	35.2
Min.	6.28	5.14	4.10	2.81	3.38	5.40	8.08	19.0	12.4	5.40	3.92	7.16
Ortalama	17.0	11.3	6.06	4.17	4.69	8.75	20.0	29.3	21.1	9.45	6.89	15.7
LT/SN/Km2	71.1	47.4	25.3	17.5	19.6	36.6	83.7	122.	88.1	39.5	28.8	65.5
AKIM mm.	190.	123.	67.9	46.8	47.5	98.0	217.	328.	228.	106.	77.2	170.
MİL. M3	45.5	29.4	16.2	11.2	11.3	23.4	51.8	78.4	54.6	25.3	18.4	40.6

SU YILI (2006) YILLIK TOPLAM AKIM 406.10 MİLYON M3 1699 MM. 53.9 LT/SN/Km2

22. Dogu Karadeniz Havzasi

D22A064 PAZAR S. KOVANLIK

YERİ : **GİRESUN - ORDU YOLUNDA BULANCAKTAN SONRA KOVANLIK KÖYÜNDEDİR.**
38°7'45" Doğu - 44°40'0" Kuzey

YAĞIŞ ALANI : **378,00 km2** **YAKLAŞIK KOT : 550 m**

GÖZLEM SÜRESİ : **01.01.1980 - 31.03.2006**

ORTALAMA AKIMLAR : **Gözlem süresinde 7.398 m3/sn. (26 Yıllık) 2006 Su yılında ---- m3/sn.**

ANLIK EN ÇOK VE EN AZ AKIMLAR:

2006 Su yılında anlık encok akım	:	**----- m3/sn**	
2006 Su yılında anlık enaz akım	:	**----- m3/sn**	
Gözlem süresinde anlık encok akım	:	**164. m3/sn**	**04.04.2003**
Gözlem süresinde anlık enaz akım	:	**0.280 m3/sn**	**20.09.1994**

Akımlar 01 Ekim 2005 'den 30 Eylül 2006' a kadar m3/sn olarak

Gün	Ekim	Kasım	Aralık	Ocak	Şubat	Mart	Nisan	Mayıs	Haziran	Temmuz	Ağustos	Eylül
01	7.10	18.5	19.7	6.08	3.92	17.7	-----	-----	-----	-----	-----	-----
02	3.92	9.17	17.3	6.42	3.92	18.1	-----	-----	-----	-----	-----	-----
03	5.16	16.1	14.9	5.40	3.92	18.5	-----	-----	-----	-----	-----	-----
04	26.0	15.7	14.5	5.74	3.92	19.7	-----	-----	-----	-----	-----	-----
05	12.5	15.7	11.8	6.08	4.20	15.3	-----	-----	-----	-----	-----	-----
06	11.8	16.1	10.7	7.78	4.68	14.9	-----	-----	-----	-----	-----	-----
07	12.5	20.5	10.3	8.12	5.40	16.5	-----	-----	-----	-----	-----	-----
08	10.3	32.8	8.46	7.44	5.16	23.7	-----	-----	-----	-----	-----	-----
09	5.74	29.0	8.12	7.44	4.44	27.5	-----	-----	-----	-----	-----	-----
10	4.92	20.1	7.44	6.76	6.42	22.3	-----	-----	-----	-----	-----	-----
11	3.92	17.7	7.44	5.40	7.44	17.7	-----	-----	-----	-----	-----	-----
12	3.92	14.5	5.40	5.40	8.12	16.5	-----	-----	-----	-----	-----	-----
13	3.64	13.7	4.92	4.44	8.12	15.7	-----	-----	-----	-----	-----	-----
14	3.36	11.4	4.68	3.92	7.78	16.9	-----	-----	-----	-----	-----	-----
15	3.36	10.3	4.68	3.92	7.44	21.4	-----	-----	-----	-----	-----	-----
16	6.42	9.91	4.68	3.92	7.44	16.1	-----	-----	-----	-----	-----	-----
17	28.5	11.0	4.68	3.36	7.78	18.5	-----	-----	-----	-----	-----	-----
18	23.2	9.54	4.92	3.64	8.12	18.9	-----	-----	-----	-----	-----	-----
19	27.0	8.12	5.16	3.92	8.12	17.7	-----	-----	-----	-----	-----	-----
20	26.0	8.46	7.44	3.92	8.80	14.5	-----	-----	-----	-----	-----	-----
21	24.1	11.8	5.40	3.92	8.12	13.7	-----	-----	-----	-----	-----	-----
22	19.3	11.4	4.92	4.44	8.12	13.7	-----	-----	-----	-----	-----	-----
23	18.5	7.10	5.40	4.44	8.80	13.7	-----	-----	-----	-----	-----	-----
24	16.5	6.76	7.78	4.20	9.91	16.5	-----	-----	-----	-----	-----	-----
25	18.1	7.44	8.46	3.92	11.0	21.4	-----	-----	-----	-----	-----	-----
26	18.1	7.44	8.46	3.92	13.3	21.4	-----	-----	-----	-----	-----	-----
27	16.5	8.80	6.42	3.92	16.1	21.4	-----	-----	-----	-----	-----	-----
28	16.5	18.9	5.40	3.92	16.9	20.5	-----	-----	-----	-----	-----	-----
29	18.1	20.5	5.40	3.92	-----	18.1	-----	-----	-----	-----	-----	-----
30	18.9	20.5	5.74	3.92	-----	16.9	-----	-----	-----	-----	-----	-----
31	19.7	-----	6.08	3.92	-----	16.9	-----	-----	-----	-----	-----	-----
Maks.	57.5	35.0	19.7	8.12	17.3	28.0	--	--	--	--	--	--
Min.	2.64	6.08	4.68	3.36	3.92	13.3	--	--	--	--	--	--
Ortalama	14.0	14.3	7.96	4.95	7.76	18.1	--	--	--	--	--	--
LT/SN/Km2	37.0	37.8	21.1	13.1	20.5	48.0	--	--	--	--	--	--
AKIM mm.	99.1	98.0	56.4	35.1	49.7	129.	--	--	--	--	--	--
MİL. M3	37.5	37.1	21.3	13.3	18.8	48.6	--	--	--	--	--	--

SU YILI (2006)

22. Dogu Karadeniz Havzasi

D22A067 SAP D. DURAKKÖYÜ

YERİ : ORDU-ULUBEY YOLUNUN 15. KM SİNDEN SOLA MELET IRMAĞI YOLUNA DÖNÜLÜR. 7 KM GİDİLDİKTEN SONRA SAĞA DÖNÜLEREK DURAK KÖYÜ İSTİKAMETİNDE, SAP DERESİ ÜZERİNDEKİ KÖPRÜNÜN MANSABINDADIR. 25

LİK PAFTADAKİ YERİ: G39-B4

37°48'1" Doğu - 40°50'4" Kuzey

YAĞIŞ ALANI : 332,00 km2 YAKLAŞIK KOT : 141 m

GÖZLEM SÜRESİ : 21.07.1981 - 30.09.2006

ORTALAMA AKIMLAR : Gözlem süresinde 7.010 m3/sn. (21 Yıllık) 2006 Su yılında ---- m3/sn.

ANLIK EN ÇOK VE EN AZ AKIMLAR:

2006 Su yılında anlık ençok akım : ----- m3/sn

2006 Su yılında anlık enaz akım : ----- m3/sn

Gözlem süresinde anlık ençok akım : 450. m3/sn 07.07.1983

Gözlem süresinde anlık enaz akım : 0.330 m3/sn 15.08.1983

20. Anahtar Eğrisi (Seviyeler cm olarak)

Seviye	Akım	Seviye	Akım	Seviye	Akım	Seviye	Akım
70	0.020	104	0.400	136	2.3	200	33.0
84	0.100	114	0.660	142	3.5	250	80.0
90	0.160	122	0.980	150	5.0	300	140.
94	0.220	126	1.2	160	7.2	350	210.
98	0.290	130	1.6	180	18.0	400	300.

Akımlar 01 Ekim 2005 'den 30 Eylül 2006' a kadar m3/sn olarak

Gün	Ekim	Kasım	Aralık	Ocak	Şubat	Mart	Nisan	Mayıs	Haziran	Temmuz	Ağustos	Eylül
01	-----	-----	3.30	9.40	3.80	12.2	6.96	8.52	2.19	6.72	1.30	1.43
02	-----	-----	3.30	8.96	3.80	11.6	27.4	9.84	2.19	27.4	1.30	1.30
03	-----	-----	3.50	11.2	4.10	12.9	45.0	14.2	2.19	21.2	1.30	1.25
04	-----	-----	3.50	11.2	5.00	15.4	30.2	11.2	2.08	7.64	1.30	1.25
05	-----	-----	3.65	9.84	6.00	9.40	28.1	9.84	1.96	5.60	1.30	1.30
06	-----	-----	3.30	13.5	7.20	8.08	26.0	11.2	1.96	12.9	1.30	1.43
07	-----	-----	3.30	14.8	18.0	8.96	22.8	11.6	1.96	14.8	1.25	1.55
08	-----	-----	3.30	22.0	9.40	10.7	22.0	11.6	1.96	9.84	1.25	1.85
09	-----	-----	3.30	14.2	9.40	9.84	21.2	12.9	1.96	5.60	1.25	1.96
10	-----	-----	3.30	10.7	7.64	6.48	21.2	12.2	1.96	4.10	1.25	1.96
11	-----	-----	3.30	8.52	16.7	5.60	19.6	9.84	1.96	3.65	1.20	2.19
12	-----	-----	3.65	8.08	18.8	5.40	18.0	7.64	3.30	3.30	1.20	8.96
13	-----	-----	3.80	8.08	11.2	5.40	16.7	6.72	2.50	3.10	1.20	5.60
14	-----	-----	3.30	8.08	8.08	5.40	18.0	9.40	4.10	2.70	1.20	3.50
15	-----	-----	3.30	7.64	6.72	10.7	18.0	8.52	4.78	2.19	1.20	3.10
16	-----	-----	3.50	6.48	6.24	7.64	19.6	6.24	3.10	1.96	1.15	2.70
17	-----	-----	3.50	6.00	5.60	6.96	21.2	14.2	3.10	1.85	1.15	2.30
18	-----	-----	3.30	6.00	8.96	7.20	21.2	8.96	2.30	1.85	1.25	1.55
19	-----	-----	3.30	4.78	31.6	10.7	22.0	6.72	1.96	2.08	1.25	1.30
20	-----	-----	4.33	3.95	21.2	10.3	22.8	5.60	1.55	2.08	1.25	1.30
21	-----	-----	3.95	3.65	16.7	8.08	24.4	4.78	1.43	1.96	1.25	1.30
22	-----	-----	3.95	3.65	15.4	6.72	24.4	4.33	1.30	1.96	1.25	1.30
23	-----	-----	4.10	4.10	13.5	6.00	26.0	4.10	1.30	1.96	1.25	1.85
24	-----	-----	4.33	3.80	13.5	6.48	28.1	3.95	1.30	1.85	1.25	1.85
25	-----	-----	4.55	3.80	18.8	24.4	29.5	3.80	1.25	1.55	1.25	2.50
26	-----	-----	4.33	3.80	19.6	16.1	13.5	3.65	1.25	1.55	1.25	3.95
27	-----	-----	4.33	3.80	18.0	13.5	9.40	4.10	1.25	1.55	1.25	2.50
28	-----	-----	5.00	3.80	12.9	11.6	8.08	4.10	1.25	1.55	1.30	1.55
29	-----	-----	6.72	3.65	-----	8.96	7.20	3.50	1.55	1.70	1.30	1.43
30	-----	-----	6.72	3.80	-----	7.20	8.96	3.10	23.6	1.85	1.30	1.43
31	-----	-----	6.24	3.80	-----	6.48	-----	2.50	-----	1.43	1.43	-----
Maks.	--	--	8.52	25.2	40.0	32.3	56.0	18.0	59.0	42.0	1.43	9.40
Min.	--	--	3.30	2.90	3.80	5.20	5.80	2.19	1.25	1.30	1.10	1.25
Ortalama	--	--	3.98	7.58	12.1	9.56	20.9	7.70	2.82	5.14	1.26	2.25
LT/SN/Km2	--	--	12.0	22.8	36.3	28.8	63.0	23.2	8.49	15.5	3.78	6.77
AKIM mm.	--	--	32.1	61.2	87.9	77.1	163.	62.2	22.0	41.5	10.1	17.6
MİL. M3	--	--	10.6	20.3	29.2	25.6	54.2	20.6	7.30	13.8	3.36	5.83

SU YILI (2006)

22. Dogu Karadeniz Havzasi

D22A073 YAGLİ D. TUGLACİK

YERİ : **TRABZON - GİRESUN YOLUNDA ESPİYEDEN SONRAKİ YALIDERENİN TUĞLACIK KÖYÜNDEDİR. 39°38'20" Doğu - 40°45'30" Kuzey**

YAĞIŞ ALANI : **398,00 km2** **YAKLAŞIK KOT : 400 m**

GÖZLEM SÜRESİ : **01.10.1981 - 30.09.2006**

ORTALAMA AKIMLAR : **Gözlem süresinde 9.795 m3/sn. (15 Yıllık) 2006 Su yılında 12.060 m3/sn.**

ANLIK EN ÇOK VE EN AZ AKIMLAR:

2006 Su yılında anlık ençok akım	:	**77.1**	**m3/sn**	**08.05.2006**
2006 Su yılında anlık enaz akım	:	**1.65**	**m3/sn**	**03.10.2005**
Gözlem süresinde anlık ençok akım	:	**202.**	**m3/sn**	**20.06.2002**
Gözlem süresinde anlık enaz akım	:	**1.00**	**m3/sn**	**30.08.2003**

Akımlar 01 Ekim 2005 'den 30 Eylül 2006' a kadar m3/sn olarak

Gün	Ekim	Kasım	Aralık	Ocak	Şubat	Mart	Nisan	Mayıs	Haziran	Temmuz	Ağustos	Eylül
01	2.72	19.2	14.9	5.68	3.58	13.9	28.0	34.0	12.3	5.68	3.58	2.27
02	2.27	15.5	13.4	5.68	3.58	13.9	33.0	36.0	11.8	24.0	3.20	2.56
03	2.27	13.4	13.4	5.40	3.96	14.9	28.0	41.0	10.7	21.6	3.20	2.56
04	13.4	11.8	12.8	5.40	3.96	17.6	24.0	34.0	9.86	12.3	3.20	2.72
05	7.88	14.4	11.2	5.68	4.15	13.4	20.0	32.0	9.44	9.44	3.04	2.72
06	4.40	19.2	9.44	6.80	4.65	13.4	15.5	36.0	9.02	9.44	3.04	2.72
07	3.77	19.2	8.24	6.80	7.16	16.0	15.5	46.4	8.60	9.86	3.04	3.04
08	3.77	42.0	7.52	6.52	6.80	26.0	20.0	77.1	8.24	9.86	2.88	2.88
09	3.20	39.0	6.80	5.68	8.60	40.0	36.0	66.8	7.52	7.88	2.88	2.88
10	2.88	25.0	6.52	5.15	7.16	25.0	41.0	52.4	7.16	6.52	2.88	2.72
11	2.88	18.4	5.96	4.65	7.52	16.0	41.0	40.0	6.52	5.96	2.88	2.88
12	2.56	14.9	5.96	4.40	9.86	12.8	40.0	34.0	7.16	5.96	2.88	7.74
13	2.40	12.3	5.15	4.40	9.02	11.8	41.0	34.0	6.24	5.40	2.88	8.70
14	2.40	10.3	4.90	4.15	7.16	13.9	41.0	32.0	5.96	5.15	2.88	6.44
15	2.88	9.44	4.90	3.96	6.52	24.0	43.0	27.0	6.24	4.65	2.88	6.22
16	3.77	9.02	5.68	3.77	5.96	19.2	46.4	25.0	5.68	4.40	2.88	6.22
17	25.0	7.88	5.15	3.77	5.40	15.5	36.0	25.0	5.96	4.40	2.72	5.78
18	16.8	7.16	4.90	3.77	5.68	13.4	30.0	24.0	5.68	4.40	2.72	5.78
19	47.6	6.80	5.15	3.77	9.44	11.8	26.0	20.0	5.15	4.65	2.72	5.56
20	34.0	6.80	5.40	3.96	9.44	10.3	27.0	18.4	5.15	4.65	2.72	5.56
21	20.8	10.3	5.15	3.77	8.24	9.44	30.0	18.4	4.90	5.15	2.72	5.56
22	14.9	11.2	4.65	3.96	9.02	9.02	28.0	17.6	4.90	4.65	2.72	5.56
23	12.8	9.44	4.90	3.96	9.86	9.86	26.0	16.8	4.65	4.40	2.72	5.56
24	10.7	8.60	4.90	3.77	10.3	14.4	39.0	16.8	4.65	4.40	2.56	5.78
25	12.8	9.02	4.90	3.77	11.8	32.0	42.0	16.0	4.40	4.40	2.56	5.78
26	21.6	9.44	4.40	3.77	14.4	29.0	32.0	15.5	4.15	4.15	2.56	5.78
27	24.0	10.3	4.15	3.58	15.5	18.4	25.0	16.0	4.40	4.15	2.56	5.78
28	20.0	12.3	4.40	3.58	13.9	15.5	20.8	14.9	4.65	4.15	2.56	5.78
29	20.8	14.9	5.15	3.58	-----	13.9	19.2	12.8	4.40	4.15	2.40	5.56
30	19.2	18.4	5.15	3.58	-----	13.9	32.0	12.3	4.90	4.15	2.27	5.56
31	21.6	-----	5.15	3.58	-----	20.0	-----	14.4	-----	3.96	2.27	-----
Maks.	65.6	50.0	14.9	6.80	15.5	40.0	46.4	77.1	14.4	42.0	3.77	21.0
Min.	1.65	6.52	4.15	3.58	3.58	9.02	15.5	12.3	4.15	3.77	2.27	2.01
Ortalama	12.5	14.5	6.78	4.53	7.95	17.0	30.9	29.2	6.68	6.90	2.81	4.82
LT/SN/Km2	31.3	36.5	17.0	11.4	20.0	42.8	77.6	73.5	16.8	17.3	7.05	12.1
AKIM mm.	83.8	94.6	45.6	30.5	48.3	115.	201.	197.	43.5	46.4	18.9	31.4
MİL. M3	33.4	37.6	18.2	12.1	19.2	45.6	80.0	78.3	17.3	18.5	7.52	12.5

SU YILI (2006) YILLIK TOPLAM AKIM 380.22 MİLYON M3 955 MM. 30.3 LT/SN/Km2

22. Dogu Karadeniz Havzasi

D22A078 TOZKÖY D. TOZKÖY

YERİ : **RİZENİN İKİZDERE İLÇESİ ÇIKIŞINDAN SAĞA AYRILAN TOZKÖY YOLUNUN 17. KM SİNDE KÖPRÜ AYAĞINDA SOL SAHİLDEDİR.**
40°36'0" Doğu - 40°41'0" Kuzey

YAĞIŞ ALANI : **284,00 km2** **YAKLAŞIK KOT : 1000 m**

GÖZLEM SÜRESİ : **01.10.1981 - 30.09.2006**

ORTALAMA AKIMLAR : **Gözlem süresinde 8.781 m3/sn. (17 Yıllık) 2006 Su yılında 12.175 m3/sn.**

ANLIK EN ÇOK VE EN AZ AKIMLAR:

2006 Su yılında anlık ençok akım	:	**70.0**	**m3/sn**	**26.05.2006**
2006 Su yılında anlık enaz akım	:	**1.11**	**m3/sn**	**21.09.2006**
Gözlem süresinde anlık ençok akım	:	**323.**	**m3/sn**	**07.06.1996**
Gözlem süresinde anlık enaz akım	:	**1.06**	**m3/sn**	**30.09.1999**

Akımlar 01 Ekim 2005 'den 30 Eylül 2006' a kadar m3/sn olarak

Gün	Ekim	Kasım	Aralık	Ocak	Şubat	Mart	Nisan	Mayıs	Haziran	Temmuz	Ağustos	Eylül
01	3.54	16.3	6.64	2.22	1.54	1.90	4.38	27.1	39.3	33.4	10.7	1.54
02	2.54	15.0	6.64	2.22	1.54	2.06	5.26	28.5	34.8	32.7	10.7	1.54
03	2.38	13.9	6.64	2.06	1.54	2.22	5.26	29.2	40.0	33.4	10.1	1.54
04	7.60	12.3	6.64	2.06	1.42	2.22	5.26	28.5	38.5	32.0	7.60	1.54
05	7.10	11.2	7.10	2.06	1.42	2.38	5.26	29.9	40.8	32.0	5.26	1.42
06	4.80	10.7	7.10	2.06	1.30	2.38	4.80	29.9	39.3	37.8	4.80	1.42
07	3.54	10.1	7.10	2.06	1.30	2.38	4.80	33.4	42.3	35.5	4.38	1.42
08	3.54	9.60	6.64	2.06	1.30	2.38	4.80	32.7	40.8	37.8	3.96	1.42
09	3.12	9.60	5.72	2.06	1.30	3.96	6.64	33.4	39.3	37.0	3.54	1.30
10	3.12	9.10	5.26	1.90	1.30	4.80	9.10	33.4	38.5	35.5	3.54	1.30
11	2.70	8.60	4.80	1.90	1.30	4.80	13.4	34.1	38.5	33.4	3.12	1.30
12	2.54	8.10	4.38	1.90	1.30	3.96	18.3	34.1	38.5	32.0	2.70	1.30
13	2.54	7.60	3.96	1.90	1.30	3.12	31.3	34.1	38.5	30.6	2.70	1.30
14	2.38	7.10	3.54	1.78	1.30	2.70	31.3	34.8	38.5	29.2	2.54	1.30
15	5.26	6.64	3.12	1.78	1.30	2.70	32.0	34.1	38.5	27.1	2.38	1.30
16	5.26	6.64	3.12	1.78	1.30	2.70	32.0	33.4	37.8	25.0	2.38	1.30
17	22.2	5.72	3.12	1.78	1.30	2.70	32.0	35.5	37.8	23.6	2.22	1.30
18	20.2	5.72	2.70	1.78	1.30	2.54	31.3	37.0	37.8	21.5	2.22	1.30
19	15.0	5.26	2.54	1.78	1.30	2.54	26.4	36.3	37.8	19.6	2.22	1.30
20	13.9	4.38	2.54	1.78	1.30	2.38	21.5	36.3	37.8	17.6	2.22	1.30
21	12.3	4.38	2.54	1.78	1.30	2.38	22.2	37.0	37.8	17.0	2.22	1.11
22	10.7	4.38	2.54	1.78	1.30	2.38	21.5	36.3	37.8	15.7	2.22	1.11
23	9.60	4.38	2.38	1.78	1.30	2.22	21.5	37.0	37.8	15.0	2.22	1.11
24	9.60	3.96	2.38	1.78	1.30	2.06	22.2	37.0	37.8	14.5	1.90	1.11
25	9.10	3.96	2.38	1.78	1.42	2.38	22.2	38.5	37.8	13.9	1.90	1.11
26	9.60	3.96	2.38	1.78	1.54	3.96	21.5	39.3	37.8	13.4	1.90	1.11
27	10.7	3.96	2.22	1.66	1.78	3.96	18.9	37.8	37.0	12.8	1.78	1.11
28	10.7	5.26	2.22	1.54	1.90	3.96	18.9	36.3	36.3	12.3	1.78	1.11
29	11.2	5.72	2.22	1.54	-----	3.96	18.3	36.3	37.0	12.3	1.66	1.11
30	11.2	6.64	2.22	1.54	-----	5.26	19.6	36.3	35.5	11.8	1.66	1.11
31	12.3	-----	2.22	1.54	-----	2.22	-----	38.5	-----	11.2	1.54	-----
Maks.	34.1	16.3	7.10	2.22	1.90	6.18	32.7	70.0	52.0	37.8	11.2	1.54
Min.	2.38	3.96	2.22	1.54	1.30	1.90	3.96	19.6	23.6	11.2	1.54	1.11
Ortalama	8.07	7.67	4.03	1.85	1.39	2.95	17.7	34.4	38.3	24.4	3.55	1.28
LT/SN/Km2	28.4	27.0	14.2	6.52	4.88	10.4	62.4	121.	135.	85.9	12.5	4.52
AKIM mm.	76.1	70.0	38.0	17.5	11.8	27.9	162.	324.	349.	230.	33.5	11.7
MİL. M3	21.6	19.9	10.8	4.96	3.35	7.91	46.0	92.1	99.2	65.4	9.51	3.33

SU YILI (2006) YILLIK TOPLAM AKIM 384.06 MİLYON M3 1352 MM. 42.9 LT/SN/Km2

22. Dogu Karadeniz Havzasi

D22A080 YAGLİ D. SINIRKÖY

YERİ : **TRABZON GİRESUN YOLUNDA ESPİYE İLÇESİNDEN SONRA SINIRKÖYDEDİR.**
38°36'30" Doğu - 40°40'30" Kuzey

YAĞIŞ ALANI : **297,00 km2** **YAKLAŞIK KOT : 750 m**

GÖZLEM SÜRESİ : **01.12.1982 – 30.09.2006**

ORTALAMA AKIMLAR : **Gözlem süresinde 6.534 m3/sn. (22 Yıllık) 2006 Su yılında 6.877 m3/sn.**

ANLIK EN ÇOK VE EN AZ AKIMLAR:

2006 Su yılında anlık ençok akım	:	**213.**	**m3/sn**	**20.10.2005**
2006 Su yılında anlık enaz akım	:	**1.74**	**m3/sn**	**28.08.2006**
Gözlem süresinde anlık ençok akım	:	**213.**	**m3/sn**	**20.10.2005**
Gözlem süresinde anlık enaz akım	:	**0.558**	**m3/sn**	**30.09.1999**

Akımlar 01 Ekim 2005 'den 30 Eylül 2006' a kadar m3/sn olarak

Gün	Ekim	Kasım	Aralık	Ocak	Şubat	Mart	Nisan	Mayıs	Haziran	Temmuz	Ağustos	Eylül
01	3.40	11.2	11.5	4.90	3.70	10.3	12.3	13.5	8.40	3.70	1.92	1.83
02	2.95	10.6	10.3	4.90	3.70	8.40	13.1	14.3	8.14	9.64	1.92	1.83
03	3.10	9.64	10.9	4.90	3.85	6.84	10.6	14.7	7.62	7.10	1.92	1.92
04	8.14	9.02	10.3	4.90	3.85	6.32	9.33	13.5	6.84	4.90	1.92	1.92
05	5.62	10.3	9.33	4.90	3.85	5.08	8.40	13.1	6.58	4.36	1.92	1.83
06	4.18	11.5	8.14	5.44	4.00	5.26	7.62	14.3	6.32	4.72	1.83	1.92
07	3.85	12.3	7.36	5.26	4.90	6.58	7.88	18.3	6.06	4.72	1.83	2.01
08	3.85	18.7	6.84	5.26	5.08	9.64	9.64	35.4	5.62	4.90	1.83	1.83
09	3.55	17.1	6.32	4.90	5.80	13.1	14.7	20.9	5.26	4.00	1.83	1.74
10	3.40	13.5	5.80	4.54	5.26	9.02	15.9	14.3	4.90	3.40	1.83	1.74
11	3.25	11.5	5.62	4.36	5.44	6.58	16.7	11.5	4.72	3.25	1.83	1.74
12	3.10	9.95	5.44	4.18	6.58	5.44	15.1	10.6	5.08	3.10	1.74	2.42
13	3.10	8.71	5.08	4.36	6.32	5.08	16.3	10.3	4.36	2.95	1.83	2.26
14	3.10	7.62	4.90	4.18	5.62	5.80	15.9	9.64	4.36	2.65	1.83	1.92
15	3.55	7.10	4.90	4.00	5.26	9.33	17.5	8.40	4.36	2.50	1.74	1.92
16	4.18	7.10	5.44	3.55	5.08	7.62	16.7	7.88	4.00	2.42	1.83	1.92
17	13.9	6.58	5.08	3.40	5.08	6.58	13.5	7.62	4.00	2.34	1.83	1.83
18	10.9	6.06	4.90	3.55	4.72	5.44	12.3	7.36	3.85	2.42	1.83	1.83
19	21.6	5.80	5.08	3.85	5.26	5.08	10.9	6.32	3.55	2.42	1.92	1.83
20	126.	5.80	5.08	3.85	5.44	4.54	11.5	5.80	3.40	2.50	1.92	1.83
21	82.1	8.71	5.08	3.70	5.44	4.18	12.3	5.80	3.40	2.65	1.92	1.83
22	36.8	9.02	4.72	3.85	5.80	4.00	11.2	5.62	3.25	2.50	1.92	1.83
23	26.4	7.62	4.90	4.00	6.58	4.54	11.2	5.62	3.25	2.42	1.92	1.83
24	13.1	7.36	4.72	3.85	6.84	6.58	14.7	5.62	3.10	2.42	1.92	2.01
25	11.5	7.36	4.72	3.85	7.88	13.1	13.9	5.44	2.95	2.34	1.92	1.83
26	9.64	7.62	4.54	3.85	9.33	11.5	11.2	5.26	2.95	2.34	1.83	1.92
27	8.71	8.40	4.18	3.85	9.95	8.71	9.64	5.44	2.95	2.26	1.83	1.83
28	9.64	10.3	4.36	3.70	9.64	7.62	8.71	4.90	3.10	2.26	1.83	1.83
29	11.5	11.9	4.72	3.55	-----	7.36	8.71	4.36	2.95	2.26	1.74	1.83
30	11.2	13.5	4.54	3.70	-----	7.62	13.1	4.36	3.25	2.18	1.74	1.83
31	11.9	-----	4.72	3.70	-----	9.64	-----	6.58	-----	2.01	1.74	-----
Maks.	213.	24.3	12.7	5.62	10.9	15.1	22.3	43.7	9.64	15.1	2.34	3.25
Min.	2.65	5.62	3.85	2.95	3.55	4.00	7.62	3.70	2.80	2.01	1.74	1.74
Ortalama	15.1	9.73	6.11	4.22	5.72	7.32	12.4	10.2	4.62	3.34	1.85	1.89
LT/SN/Km2	50.7	32.8	20.6	14.2	19.3	24.6	41.6	34.4	15.6	11.3	6.23	6.36
AKIM mm.	136.	84.9	55.1	38.0	46.6	66.0	108.	92.1	40.3	30.1	16.7	16.5
MİL. M3	40.4	25.2	16.4	11.3	13.8	19.6	32.0	27.4	12.0	8.95	4.96	4.89

SU YILI (2006) YILLIK TOPLAM AKIM 216.90 MİLYON M3 730 MM. 23.2 LT/SN/Km2

22. Dogu Karadeniz Havzasi

D22A082 SALARHA D. KÖMÜRCÜLER

YERİ : **RİZE ÇAYELİ YOLUNUN 6.KM SİNDE SAĞA AYRILAN YOLUN 13. KM SİNDE KÖMÜRCÜLER MEVKİİNDEDİR**

40°32'40" Doğu - 40°56'40" Kuzey

YAĞIŞ ALANI : **83,00 km2** **YAKLAŞIK KOT : 290 m**

GÖZLEM SÜRESİ : **01.10.1982 - 30.09.2006**

ORTALAMA AKIMLAR : **Gözlem süresinde 5.819 m3/sn. (23 Yıllık) 2006 Su yılında 3.722 m3/sn.**

ANLIK EN ÇOK VE EN AZ AKIMLAR:

2006 Su yılında anlık ençok akım	:	**109.**	**m3/sn**	**03.10.2005**
2006 Su yılında anlık enaz akım	:	**0.566**	**m3/sn**	**19.12.2005**
Gözlem süresinde anlık ençok akım	:	**458.**	**m3/sn**	**06.07.1995**
Gözlem süresinde anlık enaz akım	:	**0.566**	**m3/sn**	**19.12.2005**

Akımlar 01 Ekim 2005 'den 30 Eylül 2006' a kadar m3/sn olarak

Gün	Ekim	Kasım	Aralık	Ocak	Şubat	Mart	Nisan	Mayıs	Haziran	Temmuz	Ağustos	Eylül
01	1.50	6.52	2.94	2.13	0.980	6.52	4.40	4.40	1.03	16.5	3.20	1.08
02	1.17	4.40	2.22	1.58	1.12	7.18	3.92	4.80	1.03	14.3	2.65	1.12
03	17.5	3.92	2.22	1.28	1.33	6.74	3.92	6.52	0.980	12.1	2.43	2.10
04	14.3	3.36	1.80	1.17	1.65	6.74	3.36	6.08	0.896	10.0	2.02	4.52
05	9.62	6.96	1.58	1.12	1.73	4.60	2.94	4.60	0.854	11.2	1.70	6.52
06	8.28	8.78	1.39	2.05	1.80	5.00	2.80	3.92	0.938	12.1	1.58	4.08
07	11.6	5.86	1.28	1.50	3.78	5.00	2.94	3.64	0.854	11.5	1.40	10.0
08	8.06	31.0	1.12	3.36	3.08	10.7	4.60	3.64	0.854	13.7	1.29	12.4
09	5.00	18.2	1.08	3.78	4.06	9.34	6.52	3.22	0.812	14.3	1.23	4.08
10	2.80	6.74	0.980	2.13	2.80	5.20	5.00	2.80	0.938	8.80	1.64	2.65
11	2.80	4.20	1.03	1.58	4.80	3.64	4.60	2.60	1.44	6.52	1.34	2.10
12	2.80	8.50	1.17	1.28	4.80	3.50	4.20	2.40	1.39	5.18	1.29	1.78
13	2.13	3.50	0.938	1.17	3.22	3.22	4.20	2.60	1.22	4.74	1.29	8.80
14	2.05	3.50	0.854	1.50	2.30	4.06	4.06	9.62	1.03	3.86	1.34	10.9
15	3.64	3.50	0.770	1.39	1.88	4.80	3.92	4.60	1.03	3.64	1.29	5.68
16	3.78	2.30	0.812	1.22	1.65	3.64	3.64	3.36	1.08	4.30	1.46	10.0
17	14.3	2.05	0.770	1.12	1.50	3.08	2.70	3.08	1.88	3.09	1.23	10.6
18	7.62	1.88	0.702	1.03	1.50	2.60	2.50	2.80	1.80	2.76	1.18	4.74
19	20.1	1.73	0.634	1.03	6.30	2.80	2.30	2.60	1.39	2.76	1.18	3.20
20	18.6	1.58	1.12	1.39	4.20	2.94	2.70	2.30	1.28	4.74	2.10	2.76
21	7.84	1.73	1.12	1.39	3.08	2.70	2.70	2.13	1.17	6.24	1.18	2.32
22	5.20	2.22	0.938	1.22	3.36	2.60	2.40	1.96	1.12	5.68	1.18	2.02
23	3.92	2.60	0.896	1.12	3.78	2.80	2.40	1.88	1.12	4.30	2.02	2.21
24	3.22	2.05	1.03	1.03	3.92	5.00	5.86	1.58	1.12	3.42	1.18	1.94
25	2.80	2.22	1.28	0.938	5.64	4.20	9.90	1.44	1.22	2.98	1.08	1.64
26	3.92	2.80	1.12	0.938	7.62	3.50	4.80	1.22	1.39	2.76	1.18	1.52
27	2.80	2.40	1.08	0.938	7.84	2.60	3.22	1.73	1.80	2.54	1.12	17.9
28	10.2	2.30	0.980	0.938	5.86	2.50	2.80	1.73	1.65	2.43	1.08	8.50
29	15.6	1.88	1.03	0.896	-----	2.70	2.80	1.28	1.39	2.98	1.08	3.86
30	7.40	5.86	1.08	0.896	-----	3.08	7.84	1.17	3.78	4.96	1.03	2.54
31	6.30	-----	1.08	0.854	-----	3.22	-----	1.12	-----	4.96	1.18	-----
Maks.	109.	52.2	3.78	5.42	11.9	20.1	16.9	18.6	11.3	25.0	3.20	59.4
Min.	0.980	1.28	0.566	0.812	0.854	2.22	1.88	0.938	0.770	2.21	0.944	1.03
Ortalama	7.32	5.15	1.19	1.42	3.41	4.39	4.00	3.12	1.28	6.75	1.49	5.12
LT/SN/Km2	88.2	62.1	14.4	17.1	41.1	52.9	48.2	37.6	15.5	81.4	17.9	61.7
AKIM mm.	236.	161.	38.6	45.8	99.5	142.	125.	101.	40.1	218.	48.0	160.
MİL. M3	19.6	13.4	3.20	3.80	8.26	11.8	10.4	8.37	3.33	18.1	3.99	13.3

SU YILI (2006) YILLIK TOPLAM AKIM 117.55 MİLYON M3 1416 MM. 44.8 LT/SN/Km2

22. Dogu Karadeniz Havzasi

D22A083 KODİLI Ç. GÜMÜSKAYA

YERİ : **TRABZON GÜMÜŞHANE YOLUNUN 105. KM SİNDEN SAĞA AYRILAN YOLUN 10. KM SİNDEDİR. 39°21'0" Doğu - 40°21'0" Kuzey**

YAĞIŞ ALANI : **411,00 km2** **YAKLAŞIK KOT : 1150 m**

GÖZLEM SÜRESİ : **01.10.1982 - 30.09.2006**

ORTALAMA AKIMLAR : **Gözlem süresinde 5.938 m3/sn. (12 Yıllık) 2006 Su yılında 7.345 m3/sn.**

ANLIK EN ÇOK VE EN AZ AKIMLAR:

2006 Su yılında anlık ençok akım	**:**	**82.7**	**m3/sn**	**02.05.2006**
2006 Su yılında anlık enaz akım	**:**	**0.690**	**m3/sn**	**05.08.2006**
Gözlem süresinde anlık ençok akım	**:**	**184.**	**m3/sn**	**22.04.2005**
Gözlem süresinde anlık enaz akım	**:**	**0.230**	**m3/sn**	**01.09.1985**

Akımlar 01 Ekim 2005 'den 30 Eylül 2006' a kadar m3/sn olarak

Gün	Ekim	Kasım	Aralık	Ocak	Şubat	Mart	Nisan	Mayıs	Haziran	Temmuz	Ağustos	Eylül
01	1.18	14.4	4.40	1.66	1.44	6.60	21.6	44.5	12.0	3.30	0.810	2.36
02	1.06	8.40	3.63	1.66	1.44	6.80	24.3	50.0	11.8	2.95	0.750	2.51
03	1.55	6.80	3.63	1.66	1.55	5.68	23.6	62.0	10.8	2.86	0.780	2.60
04	2.36	5.84	3.96	1.72	1.66	12.0	18.2	45.0	10.0	2.42	0.750	2.77
05	1.55	5.68	3.63	1.84	1.72	8.40	16.1	35.3	9.80	2.23	0.720	2.68
06	1.28	5.68	3.21	1.97	1.77	8.40	14.1	45.0	10.0	2.36	1.06	2.60
07	1.18	5.04	2.77	2.03	1.90	9.60	13.3	36.2	10.5	2.60	1.39	2.68
08	1.14	4.88	2.60	2.03	2.23	12.8	17.0	49.5	9.40	2.77	1.39	1.33
09	1.06	4.40	2.42	1.97	2.51	19.2	32.6	48.0	8.20	2.51	1.66	0.810
10	1.06	3.96	2.29	1.90	2.36	12.8	36.2	31.4	7.00	2.23	2.36	0.810
11	0.984	3.63	2.23	1.77	2.36	9.00	38.9	24.0	6.00	2.03	2.86	0.810
12	0.948	3.21	2.10	1.72	2.60	7.60	39.3	20.6	5.52	1.97	2.86	0.912
13	0.912	2.77	2.03	1.72	2.51	7.00	35.3	20.6	4.88	2.03	2.68	0.948
14	0.948	2.60	1.97	1.66	2.36	7.20	34.8	18.5	5.36	1.97	2.60	0.912
15	1.77	2.36	1.90	1.66	2.29	10.0	36.6	15.2	5.36	1.84	2.68	0.876
16	1.61	2.29	1.90	1.39	2.23	9.40	32.2	14.1	5.04	1.72	2.51	0.840
17	8.20	2.16	1.97	1.44	2.03	8.40	25.0	14.7	4.88	1.55	2.60	0.840
18	5.52	2.10	1.90	1.50	2.16	7.60	22.3	15.5	4.40	1.44	2.42	0.840
19	7.80	2.03	1.90	1.50	2.51	7.20	19.2	13.0	4.29	1.39	3.21	0.840
20	3.74	1.97	1.90	1.50	2.68	6.40	19.2	12.5	4.07	1.28	2.95	0.912
21	4.40	2.10	1.90	1.50	2.68	5.68	21.6	13.0	4.07	1.18	2.95	1.02
22	3.21	2.36	1.84	1.50	3.30	5.84	20.2	13.0	3.96	1.18	2.95	1.22
23	2.60	2.42	1.84	1.50	3.85	6.80	22.6	13.6	3.85	1.18	2.77	2.51
24	2.29	2.51	1.84	1.50	4.07	7.80	60.5	13.3	4.56	1.18	2.68	1.90
25	2.03	2.60	1.90	1.50	4.72	20.2	39.8	13.6	4.56	1.14	2.60	1.84
26	1.97	2.77	1.77	1.55	5.84	20.9	27.4	14.4	3.85	1.06	2.68	1.72
27	1.84	3.04	1.66	1.61	6.20	14.7	21.6	14.7	3.52	1.02	2.60	1.55
28	1.97	3.85	1.66	1.55	5.52	12.5	17.3	12.5	3.41	0.984	2.60	1.39
29	3.12	4.29	1.66	1.55	-----	11.8	17.0	10.3	4.18	0.948	2.51	1.39
30	4.07	5.04	1.66	1.50	-----	11.8	68.1	10.8	4.18	0.912	2.60	1.44
31	18.9	-----	1.66	1.44	-----	14.7	-----	11.8	-----	0.876	2.42	-----
Maks.	41.1	21.9	5.04	2.16	7.40	29.4	82.1	82.7	15.8	3.85	4.56	2.86
Min.	0.876	1.90	1.61	1.33	1.33	5.68	12.0	9.40	2.86	0.750	0.690	0.720
Ortalama	2.98	4.04	2.31	1.65	2.80	10.2	27.9	24.4	6.31	1.78	2.21	1.53
LT/SN/Km2	7.24	9.83	5.63	4.00	6.82	24.7	67.8	59.4	15.4	4.33	5.37	3.72
AKIM mm.	19.4	25.5	15.1	10.7	16.5	66.2	176.	159.	39.8	11.6	14.4	9.64
MİL. M3	7.97	10.5	6.20	4.41	6.78	27.2	72.2	65.4	16.4	4.76	5.91	3.96

SU YILI (2006) YILLIK TOPLAM AKIM 231.69 MİLYON M3 564 MM. 17.9 LT/SN/Km2

22. Dogu Karadeniz Havzasi

D22A084 KORUM D. YAGLİDERE

YERİ : **TRABZON GÜMÜŞHANE YOLUNUN 101. KM SİNDEN SOLA AYRILAN YOLUN 13. KM SİNDEN SONRA YALIDEREDEDİR.**
39°30'0" Doğu - 40°32'50" Kuzey

YAĞIŞ ALANI : **150,00 km2** **YAKLAŞIK KOT : 1375 m**

GÖZLEM SÜRESİ : **01.11.1982 - 30.09.2006**

ORTALAMA AKIMLAR : **Gözlem süresinde 1.811 m3/sn. (14 Yıllık) 2006 Su yılında 2.362 m3/sn.**

ANLIK EN ÇOK VE EN AZ AKIMLAR:

2006 Su yılında anlık ençok akım	:	**23.9**	**m3/sn**	**31.10.2005**
2006 Su yılında anlık enaz akım	:	**0.115**	**m3/sn**	**10.08.2006**
Gözlem süresinde anlık ençok akım	:	**57.0**	**m3/sn**	**04.08.1985**
Gözlem süresinde anlık enaz akım	:	**0.090**	**m3/sn**	**01.08.1986**

Akımlar 01 Ekim 2005 'den 30 Eylül 2006' a kadar m3/sn olarak

Gün	Ekim	Kasım	Aralık	Ocak	Şubat	Mart	Nisan	Mayıs	Haziran	Temmuz	Ağustos	Eylül
01	0.344	5.52	1.36	0.520	0.312	0.824	6.12	9.62	5.28	0.732	0.160	0.130
02	0.344	2.90	1.10	0.520	0.312	0.916	6.96	13.3	4.92	0.686	0.145	0.115
03	0.344	2.18	1.10	0.480	0.280	1.10	7.20	14.8	4.56	0.686	0.145	0.130
04	0.560	1.75	1.17	0.480	0.259	1.30	6.24	13.4	3.96	0.640	0.145	0.130
05	0.560	1.49	1.30	0.440	0.259	1.10	4.80	12.5	3.60	0.560	0.145	0.130
06	0.440	1.43	1.17	0.480	0.259	1.30	4.08	13.9	3.60	0.560	0.145	0.145
07	0.408	1.30	1.05	0.440	0.259	1.75	4.08	14.2	3.50	0.640	0.130	0.145
08	0.376	1.23	0.916	0.440	0.280	2.60	4.92	15.5	3.20	0.916	0.130	0.145
09	0.344	1.10	0.824	0.408	0.312	4.92	8.11	14.3	2.70	0.640	0.130	0.145
10	0.312	1.05	0.778	0.408	0.312	2.80	11.3	11.6	2.35	0.520	0.115	0.145
11	0.280	1.05	0.732	0.376	0.312	1.75	13.9	10.2	2.18	0.480	0.115	0.145
12	0.280	1.01	0.686	0.376	0.312	1.43	14.2	9.34	1.92	0.408	0.115	0.160
13	0.280	0.916	0.686	0.376	0.344	1.30	13.6	9.34	1.69	0.376	0.115	0.175
14	0.312	0.870	0.686	0.344	0.312	1.62	13.6	9.76	1.49	0.344	0.115	0.196
15	0.520	0.824	0.640	0.312	0.312	2.26	13.6	8.64	1.36	0.344	0.115	0.217
16	2.70	0.778	0.640	0.312	0.312	1.84	13.1	7.33	1.30	0.312	0.115	0.217
17	4.08	0.732	0.686	0.312	0.344	1.75	12.1	7.46	1.30	0.312	0.115	0.217
18	1.30	0.686	0.640	0.344	0.344	1.43	11.2	8.37	1.17	0.280	0.115	0.196
19	1.62	0.686	0.640	0.344	0.344	1.43	10.0	7.20	1.10	0.280	0.115	0.196
20	1.49	0.640	0.640	0.344	0.344	1.30	9.62	6.24	1.01	0.259	0.175	0.196
21	0.870	0.686	0.600	0.312	0.376	1.10	10.5	6.12	0.916	0.238	0.175	0.196
22	0.824	0.686	0.640	0.312	0.408	1.17	10.0	6.48	0.824	0.217	0.160	0.196
23	0.778	0.686	0.600	0.344	0.480	1.23	11.5	6.96	0.778	0.196	0.145	0.259
24	0.686	0.686	0.600	0.312	0.640	1.84	20.5	7.08	0.732	0.196	0.115	0.259
25	0.640	0.732	0.600	0.312	0.732	5.04	14.9	7.08	0.778	0.175	0.115	0.259
26	0.600	0.732	0.560	0.312	0.824	5.04	10.9	6.72	0.732	0.175	0.115	0.259
27	0.600	0.778	0.480	0.312	0.824	3.60	8.11	6.84	0.686	0.175	0.130	0.259
28	0.600	1.01	0.520	0.280	0.778	3.60	6.48	6.36	0.640	0.175	0.145	0.259
29	0.778	1.10	0.520	0.259	-----	3.84	6.24	5.76	0.732	0.175	0.130	0.259
30	1.75	1.56	0.520	0.280	-----	3.96	10.7	5.40	0.824	0.175	0.130	0.259
31	16.5	-----	0.520	0.280	-----	5.04	-----	5.28	-----	0.175	0.130	-----
Maks.	23.9	6.48	1.36	0.520	0.870	5.40	23.8	16.9	5.40	1.10	0.175	0.280
Min.	0.280	0.640	0.440	0.217	0.217	0.824	3.60	5.28	0.640	0.175	0.115	0.115
Ortalama	1.34	1.23	0.761	0.367	0.400	2.26	9.95	9.26	1.99	0.389	0.132	0.191
LT/SN/Km2	8.93	8.18	5.08	2.45	2.66	15.1	66.3	61.7	13.3	2.59	0.880	1.28
AKIM mm.	23.9	21.2	13.6	6.55	6.44	40.4	172.	165.	34.5	6.94	2.36	3.31
MİL. M3	3.59	3.18	2.04	0.982	0.966	6.06	25.8	24.8	5.17	1.04	0.353	0.496

SU YILI (2006) YILLIK TOPLAM AKIM 74.48 MİLYON M3 497 MM. 15.7 LT/SN/Km2

22. Dogu Karadeniz Havzasi

D22A085 ŞENÖZ D. KAPTANPAŞA

YERİ : **RİZE ARTVİN YOLUNDA ÇAYELİNDEN SONRA KAPTANPAŞA MEVKİİNDEDİR.**
40°47'45" Doğu - 40°58'10" Kuzey

YAĞIŞ ALANI : **231,00 km2** **YAKLAŞIK KOT : 400 m**

GÖZLEM SÜRESİ : **01.02.1983 - 30.09.2006**

ORTALAMA AKIMLAR : **Gözlem süresinde 10.181 m3/sn. (21 Yıllık) 2006 Su yılında 12.173 m3/sn.**

ANLIK EN ÇOK VE EN AZ AKIMLAR:

2006 Su yılında anlık ençok akım	**:**	**114.**	**m3/sn**	**02.07.2006**
2006 Su yılında anlık enaz akım	**:**	**1.40**	**m3/sn**	**31.01.2006**
Gözlem süresinde anlık ençok akım	**:**	**205.**	**m3/sn**	**22.08.2005**
Gözlem süresinde anlık enaz akım	**:**	**0.260**	**m3/sn**	**24.11.1986**

Akımlar 01 Ekim 2005 'den 30 Eylül 2006' a kadar m3/sn olarak

Gün	Ekim	Kasım	Aralık	Ocak	Şubat	Mart	Nisan	Mayıs	Haziran	Temmuz	Ağustos	Eylül
01	6.16	22.0	18.4	3.00	2.25	10.6	10.8	22.2	12.0	16.2	14.2	2.80
02	6.88	24.0	14.8	4.00	2.25	11.8	13.2	18.6	12.6	70.7	12.1	2.80
03	10.0	19.6	13.0	4.00	2.25	13.6	12.6	19.2	12.6	53.2	11.4	3.10
04	39.0	18.4	16.0	3.50	2.25	12.4	11.4	21.0	12.6	50.8	9.40	5.20
05	20.8	16.0	14.8	3.00	2.50	11.8	9.60	18.0	12.6	53.2	8.80	9.40
06	17.2	17.2	13.0	3.50	2.50	9.04	9.00	16.8	13.2	41.2	8.20	9.40
07	16.6	20.8	11.2	9.04	2.50	9.52	9.00	16.2	13.2	38.8	7.00	17.0
08	15.4	18.4	10.6	7.60	2.75	10.6	9.00	16.2	13.8	42.8	6.40	24.0
09	12.4	36.8	9.52	7.60	3.00	18.4	13.2	18.0	13.2	35.2	6.40	11.4
10	10.6	33.0	8.56	6.88	4.72	20.8	17.4	17.4	12.6	29.6	6.40	7.60
11	9.52	25.3	8.56	4.72	4.00	14.8	16.2	16.2	12.0	25.4	5.80	6.40
12	8.56	22.0	8.08	4.72	6.16	10.6	15.6	15.0	12.0	22.6	5.80	5.80
13	7.60	25.3	8.08	4.00	7.60	9.52	15.0	14.4	14.4	20.5	4.60	11.4
14	7.60	20.8	6.88	3.00	6.88	9.52	15.0	15.6	11.4	19.1	4.60	14.2
15	12.4	18.4	6.16	3.00	4.72	10.0	15.0	18.6	10.8	20.5	4.00	9.40
16	11.8	16.0	5.44	3.00	4.00	11.2	15.6	16.8	10.2	17.0	4.60	16.3
17	22.7	14.8	6.16	2.75	4.00	10.0	15.6	15.0	9.60	16.3	4.00	19.1
18	18.4	14.2	6.16	2.50	2.50	11.8	13.2	15.0	11.4	15.6	4.00	12.1
19	33.0	13.0	5.44	2.25	2.50	11.2	12.0	15.6	12.6	18.4	4.60	8.80
20	35.7	12.4	5.44	2.25	6.16	11.2	11.4	14.4	10.8	21.2	4.60	7.60
21	29.0	11.8	5.44	3.00	4.72	11.2	12.6	13.8	9.60	20.5	4.00	5.80
22	24.0	11.8	5.44	2.25	4.00	9.52	13.8	13.8	9.00	18.4	4.00	5.80
23	20.2	11.8	4.00	3.50	4.00	10.6	13.2	14.4	8.40	17.0	4.60	7.00
24	18.4	11.2	4.00	3.00	5.44	12.4	12.6	13.8	8.40	14.9	4.60	5.20
25	17.8	10.6	4.00	2.75	6.16	12.0	11.4	15.6	7.80	14.2	4.00	5.20
26	19.6	10.0	4.00	2.75	8.08	12.6	18.0	15.0	7.20	12.8	3.70	4.00
27	17.8	11.2	4.00	2.75	11.8	12.6	14.4	15.6	8.40	12.8	3.70	19.1
28	27.9	13.0	4.00	2.75	12.4	9.60	12.0	16.2	9.60	14.2	3.70	14.9
29	30.5	15.4	3.00	2.50	-----	8.40	11.4	16.8	10.2	17.7	3.40	10.7
30	24.0	14.2	3.00	2.25	-----	9.00	10.8	14.4	9.00	17.0	3.10	8.20
31	24.6	-----	3.00	2.00	-----	9.60	-----	13.8	-----	14.9	3.10	-----
Maks.	57.6	49.2	18.4	9.52	30.0	30.0	27.0	25.8	16.2	114.	17.0	63.0
Min.	3.50	10.0	2.75	1.40	2.25	5.44	8.40	13.8	7.20	9.00	2.50	2.80
Ortalama	18.6	17.6	7.75	3.67	4.72	11.5	13.0	16.2	11.0	25.9	5.77	9.66
LT/SN/Km2	80.5	76.4	33.5	15.9	20.4	49.7	56.3	70.3	47.8	112.	25.0	41.8
AKIM mm.	215.	198.	89.8	42.6	49.4	133.	146.	188.	124.	300.	66.9	108.
MİL. M3	49.8	45.7	20.7	9.83	11.4	30.8	33.7	43.5	28.6	69.4	15.4	25.0

SU YILI (2006) YILLIK TOPLAM AKIM 383.83 MİLYON M3 1662 MM. 52.7 LT/SN/Km2

22. Dogu Karadeniz Havzasi

D22A087 Gelevera D. HASANŞEYH

YERİ : **TRABZON GİRESUN YOLUNDA CÜCE NAHİYESİNDEN SONRA HASANŞEYH KÖYÜNDEDİR.**
38°51'10" Doğu - 40°47'20" Kuzey

YAĞIŞ ALANI : **257,00 km2** **YAKLAŞIK KOT : 355 m**

GÖZLEM SÜRESİ : **01.05.1983 - 30.09.2006**

ORTALAMA AKIMLAR : **Gözlem süresinde 6.930 m3/sn. (22 Yıllık) 2006 Su yılında 5.182 m3/sn.**

ANLIK EN ÇOK VE EN AZ AKIMLAR:

2006 Su yılında anlık ençok akım	**:**	**56.3**	**m3/sn**	**19.10.2005**
2006 Su yılında anlık enaz akım	**:**	**0.549**	**m3/sn**	**17.01.2006**
Gözlem süresinde anlık ençok akım	**:**	**345.**	**m3/sn**	**20.06.1990**
Gözlem süresinde anlık enaz akım	**:**	**0.390**	**m3/sn**	**10.10.1994**

Akımlar 01 Ekim 2005 'den 30 Eylül 2006' a kadar m3/sn olarak

Gün	Ekim	Kasım	Aralık	Ocak	Şubat	Mart	Nisan	Mayıs	Haziran	Temmuz	Ağustos	Eylül
01	2.20	5.48	5.24	1.26	0.680	5.42	14.2	17.8	8.00	3.40	1.55	0.918
02	1.80	4.48	3.70	1.20	0.680	5.24	15.0	18.7	10.6	12.2	1.47	0.976
03	1.90	3.96	4.48	1.20	0.680	5.84	11.9	21.5	9.60	9.92	1.39	1.09
04	8.68	3.34	4.22	1.20	0.680	6.32	9.92	17.8	8.96	5.84	1.31	1.09
05	5.72	4.48	3.34	1.26	0.680	4.88	9.60	16.4	8.32	4.36	1.31	1.03
06	2.80	5.96	2.68	1.55	0.744	5.42	7.76	18.7	8.00	4.19	1.15	1.03
07	2.44	5.96	2.20	1.48	1.20	7.28	7.76	24.4	8.00	4.19	1.15	1.39
08	2.20	14.0	1.90	1.40	1.13	10.9	10.6	40.8	7.28	5.24	1.09	1.15
09	2.00	10.1	1.70	1.20	1.26	11.9	20.4	35.2	6.56	4.36	1.09	1.03
10	1.70	5.96	1.55	1.07	1.07	7.04	23.3	26.2	5.84	3.40	1.09	0.976
11	1.20	5.00	1.48	0.872	1.40	4.88	20.9	19.2	5.42	2.98	1.09	0.976
12	1.63	3.96	1.40	0.936	1.55	4.19	19.2	16.4	5.42	2.74	1.09	1.09
13	1.48	2.80	1.20	1.00	1.26	4.19	21.5	15.9	4.70	2.50	1.03	1.91
14	1.13	2.44	1.20	0.936	1.13	6.08	22.7	15.0	4.53	2.30	1.03	1.39
15	1.33	2.20	1.20	0.872	1.07	9.28	26.2	12.9	4.70	2.10	1.03	1.23
16	1.48	2.00	1.20	0.680	0.936	6.80	25.6	12.5	4.36	2.00	1.03	1.15
17	10.1	1.80	1.13	0.581	0.808	5.84	18.7	12.2	4.36	1.91	1.03	1.15
18	8.34	1.63	1.07	0.647	1.13	4.88	16.9	11.9	4.02	1.82	1.03	1.03
19	25.2	1.55	1.13	0.647	1.63	4.36	15.0	10.2	3.70	1.82	1.03	1.03
20	12.0	1.55	1.13	0.744	1.48	3.85	15.4	9.60	3.40	1.82	1.03	1.09
21	6.92	2.00	1.13	0.647	1.40	3.55	15.9	9.28	3.25	1.82	1.39	1.15
22	5.24	2.20	1.00	0.744	1.40	3.55	15.0	8.96	2.98	1.82	1.15	1.09
23	4.48	1.90	1.07	0.872	1.63	4.02	14.2	8.64	2.98	1.82	1.09	1.03
24	3.96	1.80	1.07	0.744	1.70	6.08	20.4	8.64	2.98	1.82	1.03	0.976
25	3.70	1.90	1.07	0.744	2.32	14.5	22.1	8.32	2.86	1.82	1.03	0.976
26	9.70	2.20	1.00	0.680	3.16	12.5	16.4	8.00	2.62	1.73	1.03	0.976
27	6.92	2.98	0.808	0.680	3.52	8.00	13.5	8.32	2.62	1.64	1.03	0.976
28	8.00	5.48	0.808	0.680	2.98	7.04	11.5	7.76	2.62	1.55	1.03	0.976
29	9.70	5.96	1.00	0.647	-----	6.80	10.9	7.04	2.50	1.55	0.976	1.03
30	6.92	8.00	0.936	0.647	-----	6.80	16.4	6.80	2.98	1.73	0.976	1.03
31	5.96	-----	1.00	0.680	-----	10.6	-----	7.76	-----	1.64	0.976	-----
Maks.	56.3	20.3	6.92	1.70	4.48	19.2	35.9	51.6	16.9	17.3	4.88	2.20
Min.	1.13	1.48	0.680	0.549	0.680	3.25	7.28	6.56	2.50	1.55	0.976	0.918
Ortalama	5.38	4.10	1.74	0.919	1.40	6.71	16.3	14.9	5.14	3.16	1.12	1.10
LT/SN/Km2	20.9	16.0	6.78	3.58	5.46	26.1	63.4	58.1	20.0	12.3	4.36	4.27
AKIM mm.	56.1	41.4	18.2	9.58	13.2	69.9	164.	156.	51.8	33.0	11.7	11.1
MİL. M3	14.4	10.6	4.67	2.46	3.40	18.0	42.2	40.0	13.3	8.47	3.00	2.85

SU YILI (2006) YILLIK TOPLAM AKIM 163.35 MİLYON M3 636 MM. 20.2 LT/SN/Km2

22. Dogu Karadeniz Havzasi

D22A089 BALLI D. KÜÇÜKKÖY

YERİ : **TRABZON ARIVİN YOLUNUN ARHAVI İLÇESİNDEN SAĞA AYRILAN KAPİSTRE YOLUNUN 12. KM SİNDEDIR**

41°21'50" Doğu - 41°15'52" Kuzey

YAĞIŞ ALANI : **66,37 km2** **YAKLAŞIK KOT : 400 m**

GÖZLEM SÜRESİ : **01.05.1984 - 30.09.2006**

ORTALAMA AKIMLAR : **Gözlem süresinde 4.101 m3/sn. (19 Yıllık) 2006 Su yılında 4.244 m3/sn.**

ANLIK EN ÇOK VE EN AZ AKIMLAR:

2006 Su yılında anlık ençok akım	**:**	**64.8**	**m3/sn**	**05.10.2005**
2006 Su yılında anlık enaz akım	**:**	**1.02**	**m3/sn**	**01.10.2005**
Gözlem süresinde anlık ençok akım	**:**	**79.7**	**m3/sn**	**21.08.2005**
Gözlem süresinde anlık enaz akım	**:**	**0.430**	**m3/sn**	**13.01.2001**

Akımlar 01 Ekim 2005 'den 30 Eylül 2006' a kadar m3/sn olarak

Gün	Ekim	Kasım	Aralık	Ocak	Şubat	Mart	Nisan	Mayıs	Haziran	Temmuz	Ağustos	Eylül
01	1.02	9.05	3.87	1.84	1.84	3.68	5.92	6.16	8.18	5.20	2.94	1.34
02	1.02	5.68	4.25	1.84	1.84	4.63	5.01	7.12	8.18	9.34	2.94	1.34
03	1.34	5.01	5.92	1.84	1.84	3.87	4.44	7.36	7.36	18.5	2.94	1.34
04	19.2	4.44	4.06	1.84	1.84	4.63	3.68	6.64	6.88	8.76	2.94	2.12
05	29.8	4.06	2.94	1.84	1.84	2.94	3.49	6.88	6.64	6.40	2.94	2.40
06	12.0	4.63	2.40	1.84	1.84	3.68	3.68	8.47	6.64	6.40	2.76	6.88
07	10.5	3.87	2.12	1.84	1.84	3.87	4.06	9.34	8.76	6.40	2.76	6.16
08	8.47	16.0	1.98	1.84	1.84	4.82	5.68	8.18	6.64	5.20	2.76	2.12
09	5.20	8.47	1.98	1.84	1.84	6.40	7.60	7.89	5.68	6.64	1.98	1.70
10	4.25	5.01	1.98	1.84	2.12	5.20	7.89	7.12	5.01	4.82	1.46	1.70
11	3.49	5.01	1.98	1.84	2.76	2.76	9.05	6.40	4.44	4.25	1.46	1.70
12	3.30	11.1	1.98	1.84	1.98	2.94	7.89	6.88	5.20	3.68	1.46	2.26
13	3.30	5.01	1.98	1.84	1.84	3.12	7.89	7.89	4.25	5.01	1.46	2.94
14	2.94	3.87	1.84	1.84	1.84	3.49	7.89	10.2	4.44	3.12	1.46	1.70
15	5.20	1.58	1.84	1.84	1.84	4.44	8.18	6.88	4.06	4.44	1.46	2.12
16	3.87	2.94	1.84	1.84	1.84	3.68	8.47	6.40	3.87	3.30	1.46	2.40
17	8.47	2.76	1.84	1.84	1.84	3.12	6.16	9.34	3.87	2.94	1.46	2.58
18	6.40	2.58	1.84	1.84	1.84	2.94	5.92	8.47	4.44	2.94	1.46	1.70
19	10.5	2.40	1.84	1.84	3.12	2.94	5.44	7.12	4.06	3.68	2.12	1.70
20	12.6	2.26	1.84	1.84	1.98	2.76	6.64	7.60	3.30	4.25	1.46	1.70
21	14.9	2.40	1.84	1.84	1.84	2.58	9.34	7.89	3.30	4.25	1.46	1.70
22	7.89	2.76	1.84	1.84	1.84	2.76	6.88	7.89	3.30	4.06	1.46	1.70
23	5.92	2.40	1.84	1.84	2.12	2.94	6.40	7.60	3.30	3.30	1.46	1.70
24	5.20	2.12	1.84	1.84	2.26	5.20	7.60	7.60	3.30	3.12	1.46	1.70
25	4.82	2.26	1.84	1.84	2.58	5.68	8.47	9.05	3.12	3.12	1.46	1.70
26	6.64	2.94	1.84	1.84	3.49	4.82	5.44	9.34	3.87	2.94	1.46	1.70
27	5.44	3.49	1.84	1.84	3.68	3.49	4.44	8.47	3.87	2.94	1.46	1.70
28	22.9	4.44	1.84	1.84	3.30	2.94	4.44	7.89	3.68	2.94	1.46	1.70
29	13.5	3.30	1.84	1.84	-----	3.30	4.44	6.16	4.06	3.49	1.34	1.70
30	6.40	7.60	1.84	1.84	-----	3.68	6.88	6.64	3.49	3.30	1.34	1.70
31	7.89	-----	1.84	1.84	-----	4.06	-----	8.18	-----	3.12	1.34	-----
Maks.	64.8	29.8	7.36	2.40	4.25	8.18	12.0	13.5	11.4	42.5	10.5	45.7
Min.	1.02	1.58	1.84	1.84	1.84	2.58	3.30	5.01	2.76	2.94	1.34	1.34
Ortalama	8.21	4.65	2.28	1.84	2.17	3.79	6.31	7.71	4.91	4.90	1.85	2.16
LT/SN/Km2	124.	70.0	34.3	27.7	32.6	57.0	95.1	116.	73.9	73.8	27.9	32.6
AKIM mm.	331.	182.	91.9	74.3	79.0	153.	246.	311.	192.	198.	74.7	84.5
MİL. M3	22.0	12.0	6.10	4.93	5.24	10.1	16.4	20.7	12.7	13.1	4.96	5.61

SU YILI (2006) YILLIK TOPLAM AKIM 133.84 MİLYON M3 2017 MM. 63.9 LT/SN/Km2

22. Dogu Karadeniz Havzasi

D22A091 BOLAMAN Ç. ÇATALPINAR

YERİ : FATSA-AYBASTI YOLUNDAN ÇATALPINAR'A VARILIR. YOL ÜZERİNDEKİ KÖPRÜNÜN MENBAINDADIR
25 LİK PAFTADAKİ YERİ: G38-B2
37°27'25" Doğu - 40°52'53" Kuzey

YAĞIŞ ALANI : 784,00 km2 YAKLAŞIK KOT : 110 m

GÖZLEM SÜRESİ : 01.11.1986 - 30.09.2006

ORTALAMA AKIMLAR : Gözlem süresinde 13.307 m3/sn. (13 Yıllık) 2006 Su yılında 12.630 m3/sn.

ANLIK EN ÇOK VE EN AZ AKIMLAR:

2006 Su yılında anlık ençok akım	:	114.	m3/sn	03.04.2006
2006 Su yılında anlık enaz akım	:	0.000	m3/sn	01.10.2005
Gözlem süresinde anlık ençok akım	:	253.	m3/sn	03.03.2005
Gözlem süresinde anlık enaz akım	:	0.000	m3/sn	01.04.2005

11. Anahtar Eğrisi (Seviyeler cm olarak)

Seviye	Akım	Seviye	Akım	Seviye	Akım	Seviye	Akım
19	0.100	50	2.9	130	48.0	230	170.
22	0.160	60	5.4	150	68.0	250	202.
30	0.480	76	11.0	170	92.0	300	285.
38	1.1	90	17.5	180	105.	350	380.
44	1.8	110	30.0	200	130.	400	495.

Akımlar 01 Ekim 2005 'den 30 Eylül 2006' a kadar m3/sn olarak

Gün	Ekim	Kasım	Aralık	Ocak	Şubat	Mart	Nisan	Mayıs	Haziran	Temmuz	Ağustos	Eylül
01	KURU	KURU	8.04	17.0	8.37	42.7	28.2	19.5	21.8	14.3	2.90	2.45
02	KURU	KURU	8.04	17.0	8.37	40.1	47.0	22.7	21.8	49.9	2.90	2.45
03	KURU	KURU	8.04	14.3	8.37	41.8	71.6	17.5	21.8	40.0	2.68	2.45
04	KURU	KURU	8.04	12.4	8.37	46.2	45.0	17.0	21.2	22.1	2.45	2.45
05	KURU	KURU	8.04	11.5	9.47	30.9	20.1	17.0	21.2	19.5	2.45	2.45
06	KURU	KURU	8.04	20.1	12.0	30.9	17.5	15.7	21.2	40.0	2.45	2.45
07	KURU	KURU	8.04	20.8	25.8	36.1	15.7	16.1	21.2	30.0	2.45	2.45
08	KURU	KURU	8.04	22.1	17.5	49.0	17.5	17.5	21.2	23.4	2.45	2.13
09	KURU	KURU	8.04	14.7	20.1	41.0	20.1	20.1	21.2	20.8	2.45	2.45
10	KURU	KURU	8.04	11.5	15.7	29.2	24.0	22.1	21.2	20.8	2.45	2.45
11	KURU	KURU	7.71	9.47	35.6	27.6	24.6	16.6	21.2	17.5	2.45	2.45
12	KURU	KURU	7.71	8.70	44.0	27.1	22.1	13.4	21.2	15.2	2.45	2.45
13	KURU	KURU	7.71	8.70	26.4	27.1	19.5	13.4	21.2	8.70	2.45	2.68
14	KURU	KURU	7.71	8.70	18.2	29.2	16.6	18.2	21.2	5.40	2.45	2.90
15	KURU	KURU	7.71	8.70	15.2	32.2	15.7	27.1	21.2	2.90	2.45	2.13
16	KURU	KURU	8.70	8.70	14.3	27.6	17.0	24.4	21.2	2.90	2.45	1.96
17	KURU	KURU	8.70	8.37	13.8	27.6	14.7	73.0	21.2	2.45	2.45	1.96
18	KURU	KURU	8.04	8.37	15.2	27.1	14.7	39.2	21.2	2.90	2.45	1.80
19	KURU	KURU	8.04	8.37	36.1	27.1	14.7	28.7	21.2	2.68	2.45	1.68
20	KURU	KURU	8.04	8.37	34.5	27.1	14.3	23.9	6.72	2.45	2.45	1.55
21	KURU	KURU	8.04	8.37	31.4	27.6	14.3	22.8	2.90	2.68	2.45	1.55
22	KURU	KURU	8.04	8.37	32.2	27.6	14.3	22.3	2.68	2.90	2.45	2.29
23	KURU	KURU	8.04	8.37	31.4	27.6	14.3	21.8	2.68	2.90	2.45	2.13
24	KURU	KURU	8.04	8.37	31.4	28.7	15.2	21.8	2.68	2.68	2.45	4.20
25	KURU	KURU	8.04	8.37	39.2	36.1	17.0	21.8	2.68	2.45	2.45	3.98
26	KURU	KURU	8.04	8.37	44.5	27.6	18.8	21.8	2.45	2.45	2.45	8.37
27	KURU	KURU	8.04	8.37	46.2	29.2	17.5	22.8	2.45	2.45	2.45	5.40
28	KURU	KURU	8.70	8.37	38.4	30.3	16.1	22.3	2.68	2.68	2.45	3.12
29	KURU	KURU	11.0	8.37	-----	29.2	14.7	21.8	2.90	2.90	2.45	2.13
30	KURU	KURU	11.0	8.37	-----	28.7	22.1	21.8	22.7	2.90	2.45	2.13
31	KURU	-----	11.0	8.37	-----	28.7	-----	21.8	-----	2.90	2.45	-----
Maks.	KURU	KURU	14.7	27.0	65.9	76.0	114.	109.	33.2	99.8	3.33	14.3
Min.	KURU	KURU	7.71	8.04	8.37	24.4	14.3	13.4	2.45	2.45	2.45	1.55
Ortalama	KURU	KURU	8.34	11.0	24.4	31.9	21.5	22.8	15.3	12.1	2.49	2.70
LT/SN/Km2	0.000	0.000	10.6	14.0	31.1	40.7	27.4	29.0	19.5	15.4	3.17	3.45
AKIM mm.	0.000	0.000	28.5	37.5	75.2	109.	71.1	77.8	50.5	41.2	8.49	8.93
MİL. M3	0.000	0.000	22.3	29.4	58.9	85.4	55.7	61.0	39.6	32.3	6.66	7.00

SU YILI (2006) YILLIK TOPLAM AKIM 398.26 MİLYON M3 508 MM. 16.1 LT/SN/Km2

22. Dogu Karadeniz Havzasi

D22A092 REŞADİYE Ç. KABATAŞ

YERİ : FATSA-AYBASTI YOLUNDAKİ ÇATAK NAHİYESİNDEN KABATAŞ MEVKİNE VARILIR. İSTASYON SAĞ SAHİLDEDİR. 25 LİK PAFTAKİ YERİ: G38-B3
37°27'31" Doğu - 40°46'35" Kuzey

YAĞIŞ ALANI : 302,50 km2 YAKLAŞIK KOT : 333 m

GÖZLEM SÜRESİ : 01.12.1986 - 30.09.2006

ORTALAMA AKIMLAR : Gözlem süresinde 6.390 m3/sn. (15 Yıllık) 2006 Su yılında ---- m3/sn.

ANLIK EN ÇOK VE EN AZ AKIMLAR:

2006 Su yılında anlık ençok akım : ----- m3/sn

2006 Su yılında anlık enaz akım : ----- m3/sn

Gözlem süresinde anlık ençok akım : 225. m3/sn 02.03.2005

Gözlem süresinde anlık enaz akım : 0.000 m3/sn 24.07.1987

11. Anahtar Eğrisi (Seviyeler cm olarak)

Seviye	Akım	Seviye	Akım	Seviye	Akım	Seviye	Akım
16	0.100	46	3.2	100	29.0	200	146.
25	0.420	54	5.3	120	46.0	250	240.
30	0.760	60	7.3	140	66.0	300	340.
35	1.3	70	11.2	160	88.0	350	460.
42	2.4	80	16.0	180	115.	400	620.

Akımlar 01 Ekim 2005 'den 30 Eylül 2006' a kadar m3/sn olarak

Gün	Ekim	Kasım	Aralık	Ocak	Şubat	Mart	Nisan	Mayıs	Haziran	Temmuz	Ağustos	Eylül
01	-----	-----	4.25	7.30	3.00	23.4	16.0	12.1	3.73	22.0	1.30	0.860
02	-----	-----	3.99	7.30	3.00	24.1	34.6	16.0	3.46	18.4	1.30	1.44
03	-----	-----	3.73	6.33	3.00	26.2	40.6	19.0	3.20	2.20	1.19	1.19
04	-----	-----	3.73	5.30	3.20	29.0	27.6	14.0	2.80	2.00	1.19	1.07
05	-----	-----	3.46	5.30	3.73	17.8	23.4	16.6	2.60	1.86	1.07	0.960
06	-----	-----	3.46	10.0	6.00	19.0	19.0	22.0	2.60	4.78	1.07	0.860
07	-----	-----	3.00	10.8	10.8	24.1	17.2	37.0	2.60	4.51	0.960	1.19
08	-----	-----	3.00	10.0	8.07	37.0	19.0	41.5	2.80	3.20	0.860	0.960
09	-----	-----	3.00	6.65	10.0	28.3	22.0	25.5	2.80	1.86	0.960	0.860
10	-----	-----	3.00	5.04	8.07	17.8	19.0	19.0	3.00	1.86	0.860	0.860
11	-----	-----	2.80	4.25	24.8	13.5	19.6	13.0	2.80	1.86	0.860	0.860
12	-----	-----	2.80	3.73	26.2	12.6	16.6	10.8	3.00	1.72	0.860	1.72
13	-----	-----	2.80	3.73	14.0	14.0	14.5	11.2	2.80	1.58	0.860	1.58
14	-----	-----	2.80	3.46	9.60	19.0	12.6	14.0	2.40	1.30	0.860	1.07
15	-----	-----	2.80	3.46	7.68	20.8	11.7	13.0	2.80	1.19	0.860	0.960
16	-----	-----	6.65	3.46	6.33	14.0	12.6	13.5	2.20	1.07	0.860	0.860
17	-----	-----	6.98	3.46	5.30	11.7	9.22	47.0	2.40	1.07	0.860	0.860
18	-----	-----	5.04	3.46	6.33	9.60	8.45	24.8	2.20	0.960	0.860	0.760
19	-----	-----	4.51	3.46	12.1	10.8	7.30	17.2	2.00	1.07	0.860	0.760
20	-----	-----	4.51	3.46	12.6	10.4	6.98	12.6	1.86	1.30	1.30	0.680
21	-----	-----	4.25	3.46	11.7	10.8	6.65	10.4	1.72	1.19	1.07	0.760
22	-----	-----	3.99	3.20	11.7	10.8	6.00	8.83	1.72	1.19	0.860	1.07
23	-----	-----	4.25	3.20	11.7	12.1	5.65	7.30	1.58	1.30	0.860	0.960
24	-----	-----	3.99	3.20	12.1	16.6	8.07	6.33	1.72	1.19	0.860	1.19
25	-----	-----	3.99	3.20	15.5	24.1	19.6	5.65	1.58	1.07	0.860	1.44
26	-----	-----	3.73	3.20	19.0	17.8	12.6	5.04	1.58	1.19	0.860	3.00
27	-----	-----	3.73	3.20	21.4	17.8	10.0	11.2	1.58	1.19	0.860	2.00
28	-----	-----	3.99	3.20	18.4	18.4	9.60	9.22	1.72	1.19	0.760	1.19
29	-----	-----	4.51	3.00	-----	16.6	8.83	6.00	1.72	1.30	0.760	0.960
30	-----	-----	4.51	3.00	-----	16.0	14.0	5.04	3.20	1.30	0.760	0.960
31	-----	-----	4.78	3.00	-----	16.0	-----	4.25	-----	1.30	0.760	-----
Maks.	--	--	10.0	12.1	45.1	53.6	48.9	84.7	15.0	524.	3.46	6.00
Min.	--	--	2.80	3.00	3.00	9.60	5.65	4.25	1.58	0.960	0.760	0.540
Ortalama	--	--	3.94	4.67	10.9	18.1	15.3	15.5	2.41	2.88	0.938	1.13
LT/SN/Km2	--	--	13.0	15.4	36.0	59.7	50.6	51.1	7.95	9.51	3.10	3.73
AKIM mm.	--	--	34.9	41.4	87.2	160.	131.	137.	20.6	25.5	8.30	9.68
MİL. M3	--	--	10.5	12.5	26.4	48.4	39.7	41.4	6.24	7.71	2.51	2.93

SU YILI (2006)

22. Dogu Karadeniz Havzasi

D22A093 TURNA Ç. CUMHURİYET KÖYÜ

YERİ : ORDU-GİRESUN YOLUNUN 5. KM ŞİNDEN SOLA AYRILAN KÖY YOLUNUN 20. KM SİNDEKİ CUMHURİYET KÖYÜNDEKİ KÖPRÜDEDİR. 25 LİK PAFTADAKİ YERİ: G39-B3
37°57'42" Doğu - 40°49'54" Kuzey

YAĞIŞ ALANI : 210,00 km2 YAKLAŞIK KOT : 375 m

GÖZLEM SÜRESİ : 06.11.1990 - 30.09.2006

ORTALAMA AKIMLAR : Gözlem süresinde 4.877 m3/sn. (10 Yıllık) 2006 Su yılında 5.622 m3/sn.

ANLIK EN ÇOK VE EN AZ AKIMLAR:

2006 Su yılında anlık ençok akım	:	84.0	m3/sn	02.07.2006
2006 Su yılında anlık enaz akım	:	0.490	m3/sn	31.08.2006
Gözlem süresinde anlık ençok akım	:	103.	m3/sn	31.07.1992
Gözlem süresinde anlık enaz akım	:	0.000	m3/sn	01.01.1990

2. Anahtar Eğrisi (Seviyeler cm olarak)

Seviye	Akım	Seviye	Akım	Seviye	Akım	Seviye	Akım
60	0.020	92	0.860	140	13.0	300	170.
72	0.100	96	1.2	160	23.0	350	260.
76	0.150	105	2.7	180	37.0	400	360.
80	0.280	115	4.7	200	54.0	460	500.
88	0.540	125	7.5	250	100.	500	600.

Akımlar 01 Ekim 2005 'den 30 Eylül 2006' a kadar m3/sn olarak

Gün	Ekim	Kasım	Aralık	Ocak	Şubat	Mart	Nisan	Mayıs	Haziran	Temmuz	Ağustos	Eylül
01	1.13	10.6	5.26	5.26	1.68	15.0	7.80	8.70	1.13	0.930	0.930	0.720
02	1.13	7.50	4.26	4.48	1.68	15.0	14.0	10.6	1.13	23.0	0.930	0.790
03	2.34	6.94	3.82	4.04	1.89	16.5	26.6	15.0	1.13	24.8	0.860	0.790
04	29.8	7.22	3.06	4.04	2.46	17.0	15.0	10.6	0.930	9.00	0.860	0.790
05	18.5	8.70	2.70	4.26	2.88	10.2	12.6	11.4	0.860	7.50	0.790	0.860
06	10.2	13.0	2.46	9.80	3.42	10.2	9.40	20.0	0.860	13.5	0.720	0.860
07	6.38	18.5	2.22	9.80	6.66	13.0	8.40	29.8	0.860	16.5	0.720	0.930
08	4.04	33.0	1.68	9.40	4.26	21.5	10.2	26.6	0.930	15.5	0.630	0.930
09	2.88	21.0	1.68	5.54	4.26	16.5	11.8	15.0	0.930	7.22	0.630	0.930
10	2.46	10.2	1.68	4.04	3.82	9.00	9.80	11.4	0.930	4.48	0.630	1.89
11	2.34	7.50	1.68	3.60	8.10	6.38	9.80	8.10	0.930	3.24	0.630	3.60
12	2.10	5.54	1.68	2.70	8.40	6.10	7.50	5.82	2.88	2.70	0.630	4.70
13	2.10	4.04	1.46	2.70	6.10	6.38	7.22	6.38	1.25	2.34	0.630	2.70
14	1.89	3.24	1.25	2.46	4.70	9.00	6.10	12.6	1.25	2.10	0.630	1.25
15	1.89	2.88	1.25	2.34	3.82	33.8	5.54	11.0	2.10	1.68	0.630	1.00
16	6.66	2.70	1.25	2.22	3.42	16.5	6.94	7.22	1.13	1.46	0.630	0.860
17	27.8	2.46	1.25	2.10	3.24	11.4	4.98	6.38	1.25	1.25	0.630	0.860
18	17.0	2.34	1.25	2.10	3.82	9.00	4.04	5.26	1.13	1.25	0.630	0.720
19	35.4	2.34	1.25	2.10	10.2	9.80	3.60	4.48	0.930	1.46	0.630	0.720
20	19.0	2.34	1.46	2.22	7.22	8.70	3.42	3.82	0.860	1.25	0.630	0.720
21	17.5	2.58	1.46	2.10	6.66	7.50	3.06	3.24	0.860	1.25	0.630	0.720
22	10.6	3.60	1.25	2.10	6.94	6.94	2.88	2.70	0.860	1.25	0.630	0.790
23	6.66	3.82	1.89	2.22	6.94	7.80	4.98	2.34	0.860	1.25	0.630	2.46
24	5.82	4.26	1.89	2.22	7.22	11.4	9.80	2.34	0.860	1.00	0.630	2.70
25	5.54	5.54	1.89	2.10	11.8	15.0	18.0	2.10	0.860	0.930	0.630	2.10
26	5.54	16.0	1.68	2.10	15.5	11.0	17.5	1.89	0.720	0.930	0.630	2.46
27	4.48	11.4	2.10	2.10	16.0	10.2	9.80	2.46	0.720	0.930	0.630	1.25
28	5.54	6.10	2.70	2.10	11.8	9.80	6.66	2.58	0.720	0.930	0.720	0.930
29	23.0	3.60	3.60	1.89	-----	7.22	6.38	2.22	0.720	1.68	0.720	0.860
30	24.2	7.22	3.60	1.68	-----	6.66	9.40	1.68	1.46	1.68	0.720	0.860
31	22.0	-----	3.42	1.68	-----	7.50	-----	1.25	-----	1.25	0.720	-----
Maks.	45.0	37.0	5.54	11.8	19.0	55.7	34.6	40.2	5.26	84.0	1.46	8.10
Min.	1.00	2.22	1.25	1.46	1.68	6.10	2.88	1.25	0.720	0.930	0.490	0.490
Ortalama	10.5	7.87	2.20	3.47	6.25	11.7	9.11	8.22	1.07	4.98	0.687	1.39
LT/SN/Km2	50.1	37.5	10.5	16.5	29.7	55.6	43.4	39.2	5.09	23.7	3.27	6.63
AKIM mm.	134.	97.2	28.0	44.2	72.0	149.	112.	105.	13.2	63.5	8.76	17.2
MİL. M3	28.2	20.4	5.88	9.29	15.1	31.3	23.6	22.0	2.77	13.3	1.84	3.61

SU YILI (2006) YILLIK TOPLAM AKIM 177.29 MİLYON M3 844 MM. 26.8 LT/SN/Km2

22. Dogu Karadeniz Havzasi

D22A095 YAYLA D. SÖGÜTAĞIL

YERİ : **GÜMÜŞHANE-KELKİT YOLU ÜZERINDE YENIYOL MEVKIINDEN 15 KM İLERİDE SAĞ SAHILDE. 40°27'0" Doğu - 39°47'0" Kuzey**

YAĞIŞ ALANI : **110,00 km2** **YAKLAŞIK KOT : 1500 m**

GÖZLEM SÜRESİ : **01.10.1998 - 30.09.2006**

ORTALAMA AKIMLAR : **Gözlem süresinde 1.073 m3/sn. (8 Yıllık) 2006 Su yılında 1.824 m3/sn.**

ANLIK EN ÇOK VE EN AZ AKIMLAR:

2006 Su yılında anlık ençok akım	**:**	**17.8**	**m3/sn**	**24.04.2006**
2006 Su yılında anlık enaz akım	**:**	**0.054**	**m3/sn**	**25.09.2006**
Gözlem süresinde anlık ençok akım	**:**	**17.8**	**m3/sn**	**24.04.2006**
Gözlem süresinde anlık enaz akım	**:**	**0.030**	**m3/sn**	**22.01.2002**

Akımlar 01 Ekim 2005 'den 30 Eylül 2006' a kadar m3/sn olarak

Gün	Ekim	Kasım	Aralık	Ocak	Şubat	Mart	Nisan	Mayıs	Haziran	Temmuz	Ağustos	Eylül
01	0.214	3.00	0.808	0.524	0.388	0.422	5.52	11.2	1.54	0.284	0.145	0.086
02	0.214	1.68	0.808	0.490	0.388	0.422	6.00	14.5	1.33	0.284	0.135	0.080
03	0.214	1.33	0.808	0.456	0.388	0.422	5.28	16.0	1.18	0.284	0.135	0.086
04	0.402	1.10	0.808	0.422	0.388	0.422	4.20	14.2	1.10	0.284	0.135	0.086
05	0.288	1.03	0.956	0.422	0.388	0.490	3.60	12.7	1.03	0.266	0.115	0.086
06	0.250	1.03	0.956	0.422	0.388	0.558	3.00	12.7	0.956	0.284	0.105	0.086
07	0.232	1.03	0.882	0.422	0.354	0.626	3.60	12.4	0.956	0.284	0.099	0.093
08	0.232	1.03	0.808	0.388	0.354	0.734	5.52	13.6	0.956	0.354	0.099	0.093
09	0.214	0.956	0.734	0.388	0.230	0.808	10.6	12.7	0.808	0.302	0.099	0.093
10	0.196	0.882	0.660	0.388	0.099	0.660	12.7	11.2	0.660	0.284	0.099	0.093
11	0.196	0.808	0.660	0.388	0.105	0.626	13.6	9.44	0.626	0.266	0.099	0.093
12	0.196	0.808	0.660	0.388	0.125	0.626	13.0	8.88	0.626	0.230	0.099	0.093
13	0.178	0.734	0.660	0.388	0.135	0.592	13.0	8.60	0.592	0.230	0.093	0.099
14	0.196	0.660	0.626	0.388	0.135	0.626	13.3	8.04	0.524	0.215	0.093	0.099
15	0.488	0.660	0.626	0.388	0.135	0.808	13.6	6.48	0.524	0.200	0.086	0.099
16	0.440	0.660	0.592	0.388	0.135	0.734	13.9	5.76	0.490	0.200	0.086	0.105
17	0.788	0.592	0.558	0.388	0.135	0.660	12.4	5.76	0.456	0.200	0.080	0.099
18	0.734	0.558	0.558	0.388	0.135	0.660	11.2	5.76	0.456	0.200	0.080	0.093
19	0.680	0.524	0.558	0.388	0.135	0.660	10.0	4.80	0.456	0.200	0.093	0.093
20	1.09	0.490	0.490	0.388	0.125	0.660	10.0	4.00	0.456	0.185	0.093	0.093
21	0.632	0.490	0.456	0.388	0.125	0.660	10.3	3.80	0.422	0.185	0.093	0.093
22	0.632	0.490	0.490	0.388	0.135	0.660	10.3	3.40	0.320	0.185	0.093	0.105
23	0.632	0.490	0.524	0.388	0.170	0.808	10.6	3.40	0.302	0.185	0.093	0.125
24	0.632	0.558	0.524	0.388	0.215	1.82	16.0	3.00	0.302	0.170	0.086	0.115
25	0.632	0.524	0.524	0.388	0.230	2.10	14.5	2.66	0.320	0.170	0.086	0.086
26	0.632	0.456	0.524	0.388	0.354	1.82	10.9	2.52	0.302	0.170	0.086	0.086
27	0.632	0.456	0.524	0.388	0.422	2.10	9.16	2.80	0.302	0.170	0.093	0.099
28	0.680	0.558	0.524	0.388	0.422	2.10	8.04	2.66	0.284	0.170	0.093	0.115
29	0.734	0.626	0.524	0.388	-----	2.24	7.20	2.10	0.284	0.170	0.093	0.145
30	1.02	0.808	0.524	0.388	-----	2.66	9.16	1.82	0.284	0.170	0.086	0.185
31	3.94	-----	0.524	0.388	-----	3.80	-----	1.68	-----	0.170	0.086	-----
Maks.	5.10	4.80	0.956	0.524	0.422	5.04	17.8	17.8	1.54	0.388	0.155	0.185
Min.	0.178	0.456	0.456	0.388	0.099	0.422	2.66	1.54	0.284	0.155	0.074	0.054
Ortalama	0.588	0.834	0.641	0.402	0.241	1.06	9.67	7.37	0.628	0.224	0.099	0.100
LT/SN/Km2	5.35	7.58	5.83	3.66	2.19	9.67	87.9	67.0	5.71	2.04	0.896	0.910
AKIM mm.	14.3	19.7	15.6	9.79	5.29	25.9	228.	180.	14.8	5.46	2.40	2.36
MİL. M3	1.58	2.16	1.72	1.08	0.582	2.85	25.1	19.7	1.63	0.601	0.264	0.259

SU YILI (2006) YILLIK TOPLAM AKIM 57.53 MİLYON M3 523 MM. 16.6 LT/SN/Km2

22. Dogu Karadeniz Havzasi

D22A096 Cimil D. KÖKNAR

YERİ : **İKİZDERE CİMİL YOLUNUN 14. KM SİNDE ESKİ ORMAN DEPOSU ÜSTÜ**
40°40'50" Doğu - 40°46'10" Kuzey

YAĞIŞ ALANI : **155,80 km2** **YAKLAŞIK KOT : 1280 m**

GÖZLEM SÜRESİ : **01.10.1999 - 30.09.2006**

ORTALAMA AKIMLAR : **Gözlem süresinde 6.196 m3/sn. (7 Yıllık) 2006 Su yılında 6.543 m3/sn.**

ANLIK EN ÇOK VE EN AZ AKIMLAR:

2006 Su yılında anlık ençok akım	:	**34.8**	**m3/sn**	**07.06.2006**
2006 Su yılında anlık enaz akım	:	**0.832**	**m3/sn**	**19.02.2006**
Gözlem süresinde anlık ençok akım	:	**58.8**	**m3/sn**	**21.06.2002**
Gözlem süresinde anlık enaz akım	:	**0.295**	**m3/sn**	**01.04.2003**

Akımlar 01 Ekim 2005 'den 30 Eylül 2006' a kadar m3/sn olarak

Gün	Ekim	Kasım	Aralık	Ocak	Şubat	Mart	Nisan	Mayıs	Haziran	Temmuz	Ağustos	Eylül
01	3.10	7.00	3.40	1.40	1.16	1.57	4.00	11.7	25.8	12.6	4.30	2.08
02	2.42	6.04	3.40	1.32	1.24	1.57	4.00	13.8	27.0	12.6	4.30	1.91
03	2.76	5.08	4.60	1.32	1.32	1.57	4.00	12.6	27.6	12.0	3.70	1.91
04	9.80	4.60	4.00	1.40	1.24	1.57	3.40	12.6	26.4	11.7	3.70	2.08
05	4.60	4.60	3.70	1.57	1.24	1.57	3.10	13.2	27.0	11.7	3.40	2.08
06	3.10	4.60	3.40	1.74	1.24	1.57	3.10	13.8	27.6	11.7	3.10	2.59
07	2.93	4.30	3.10	1.57	1.24	1.74	3.70	17.4	30.0	11.7	3.10	2.76
08	2.76	4.60	3.10	1.57	1.24	2.25	4.30	18.0	26.4	13.2	3.10	2.08
09	2.59	4.30	2.93	1.57	1.32	2.59	7.70	16.8	25.2	11.7	3.10	1.91
10	2.93	3.70	2.93	1.57	1.24	2.08	9.10	15.6	23.4	11.1	2.93	1.91
11	2.25	3.70	2.76	1.57	1.24	1.91	10.8	15.0	21.6	11.1	2.76	1.91
12	2.25	3.70	2.76	1.57	1.24	1.91	11.1	16.2	19.8	11.1	2.76	2.25
13	2.08	3.40	2.59	1.57	1.24	1.74	11.4	18.6	19.2	10.8	2.76	2.25
14	2.25	3.10	2.42	1.40	1.24	1.91	11.7	16.2	20.4	10.5	2.59	2.08
15	4.00	3.10	2.42	1.40	1.24	2.08	14.4	13.8	19.8	9.80	2.42	2.25
16	3.10	3.10	2.42	1.40	1.24	2.08	15.0	15.0	18.0	9.10	2.42	2.59
17	11.7	3.10	2.42	1.40	1.24	2.08	13.8	19.2	17.4	8.40	2.42	2.08
18	7.70	3.10	2.42	1.40	1.40	2.08	13.8	20.4	16.2	7.70	3.10	1.91
19	7.70	3.10	2.25	1.40	1.16	2.08	13.2	18.6	15.0	7.70	3.40	1.74
20	6.04	3.10	2.25	1.40	1.24	1.91	14.4	20.4	15.6	7.00	2.93	1.74
21	5.08	3.10	2.08	1.40	1.24	1.91	13.8	22.8	15.6	7.00	2.93	1.74
22	4.60	3.10	2.08	1.40	1.16	1.91	13.8	24.0	14.4	7.00	2.59	1.91
23	4.60	2.93	2.08	1.40	1.08	1.91	13.2	24.6	14.4	6.04	2.42	1.91
24	4.60	2.76	2.08	1.40	1.32	2.25	15.0	24.6	13.8	6.04	2.25	2.25
25	4.30	2.76	1.74	1.40	1.40	2.93	14.4	26.4	14.4	5.08	2.25	1.91
26	6.04	2.93	1.57	1.40	1.40	2.93	11.7	26.4	15.6	4.60	2.25	2.93
27	5.56	3.70	1.57	1.32	1.40	2.76	11.4	25.8	12.6	4.60	2.25	2.42
28	6.52	4.00	1.57	1.32	1.40	2.93	10.8	24.6	13.2	4.60	2.08	2.08
29	6.04	3.40	1.57	1.32	-----	2.93	10.8	21.0	13.2	5.08	2.08	2.08
30	5.08	3.70	1.57	1.32	-----	2.93	11.7	23.4	12.0	4.60	2.08	2.59
31	8.40	-----	1.40	1.32	-----	3.40	-----	25.2	-----	4.30	2.08	-----
Maks.	21.6	9.10	5.56	1.91	1.40	4.00	20.4	31.8	34.8	18.0	4.60	7.00
Min.	2.08	1.08	1.32	1.24	0.832	1.40	2.93	10.8	11.4	3.70	1.91	1.74
Ortalama	4.74	3.79	2.53	1.44	1.26	2.15	10.1	19.0	19.6	8.78	2.82	2.13
LT/SN/Km2	30.4	24.3	16.3	9.22	8.11	13.8	64.7	122.	126.	56.3	18.1	13.7
AKIM mm.	81.5	63.1	43.6	24.7	19.6	37.0	168.	326.	326.	151.	48.6	35.5
MİL. M3	12.7	9.82	6.79	3.85	3.06	5.76	26.1	50.8	50.9	23.5	7.56	5.52

SU YILI (2006) YILLIK TOPLAM AKIM 206.36 MİLYON M3 1325 MM. 42.0 LT/SN/Km2

22. Dogu Karadeniz Havzasi

D22A097 Maçka D. Ormanüstü

YERİ : **TRABZON-ERZURUM KARAYOLU ÜZERİNDEKI ÇATAK MEVKIINDEN 4.5 KM İLERIDEDİR**
39°32'30" Doğu - 40°48'0" Kuzey

YAĞIŞ ALANI : **169,00 km2** **YAKLAŞIK KOT : 600 m**

GÖZLEM SÜRESİ : **01.10.1999 - 30.09.2006**

ORTALAMA AKIMLAR : **Gözlem süresinde 2.265 m3/sn. (7 Yıllık) 2006 Su yılında 2.351 m3/sn.**

ANLIK EN ÇOK VE EN AZ AKIMLAR:

2006 Su yılında anlık ençok akım	:	**14.9**	**m3/sn**	**31.10.2005**
2006 Su yılında anlık enaz akım	:	**0.014**	**m3/sn**	**19.09.2006**
Gözlem süresinde anlık ençok akım	:	**22.9**	**m3/sn**	**14.04.2005**
Gözlem süresinde anlık enaz akım	:	**0.014**	**m3/sn**	**19.09.2006**

Akımlar 01 Ekim 2005 'den 30 Eylül 2006' a kadar m3/sn olarak

Gün	Ekim	Kasım	Aralık	Ocak	Şubat	Mart	Nisan	Mayıs	Haziran	Temmuz	Ağustos	Eylül
01	0.690	10.0	5.30	0.720	0.324	2.20	5.60	6.92	0.635	0.430	0.272	0.018
02	0.420	7.64	4.85	0.635	0.350	2.10	6.20	6.92	0.550	1.06	0.184	0.026
03	0.760	6.38	5.00	0.550	0.390	2.20	6.74	7.28	0.470	1.80	0.130	0.041
04	8.40	5.60	4.85	0.510	0.470	3.06	5.75	6.20	0.390	0.805	0.090	0.052
05	9.60	5.00	3.86	0.720	0.510	2.84	5.45	5.75	0.324	0.470	0.077	0.041
06	6.38	4.58	3.28	0.805	0.430	2.51	5.15	7.82	0.324	0.470	0.064	0.032
07	4.85	4.85	2.51	0.890	0.324	2.51	4.70	7.28	0.324	0.635	0.052	0.026
08	4.34	7.28	2.10	0.635	0.390	2.62	5.45	7.82	0.298	1.60	0.047	0.026
09	3.74	6.56	1.90	0.510	0.470	3.17	9.20	8.80	0.246	1.23	0.052	0.023
10	3.06	5.90	1.70	0.510	0.390	3.28	9.40	7.64	0.202	0.635	0.052	0.020
11	2.73	4.58	1.50	0.430	0.430	2.84	9.20	6.38	0.220	0.470	0.047	0.023
12	2.40	3.86	1.50	0.390	0.470	2.40	9.20	5.45	0.220	0.350	0.047	0.184
13	3.06	2.95	1.06	0.390	0.550	2.20	9.00	4.70	0.220	0.350	0.035	0.052
14	2.10	2.51	0.975	0.350	0.390	2.62	9.40	5.45	0.202	0.272	0.032	0.029
15	1.90	2.40	1.23	0.350	0.350	3.74	9.20	5.30	0.202	0.202	0.032	0.026
16	2.51	2.10	1.23	0.324	0.350	3.06	8.20	4.46	0.202	0.130	0.032	0.023
17	9.20	1.90	1.06	0.298	0.390	2.62	6.20	3.98	0.350	0.130	0.029	0.018
18	13.1	1.70	0.890	0.298	1.50	2.30	5.45	3.39	0.324	0.148	0.029	0.016
19	13.3	1.40	0.890	0.324	1.90	2.10	5.00	2.84	0.202	0.220	0.029	0.014
20	11.5	1.40	0.890	0.272	1.70	1.70	4.85	2.51	0.148	0.324	0.041	0.014
21	8.80	1.60	0.720	0.246	1.15	1.50	5.45	2.30	0.117	0.324	0.032	0.014
22	7.64	1.70	0.350	0.220	1.32	1.60	5.15	2.00	0.104	0.324	0.029	0.020
23	6.56	1.50	0.550	0.246	1.50	2.00	6.38	1.70	0.104	0.272	0.026	0.023
24	6.05	1.60	0.635	0.246	1.60	3.28	6.56	1.60	0.130	0.246	0.026	0.090
25	5.90	1.80	0.510	0.246	1.80	5.75	6.74	1.40	0.117	0.220	0.035	0.052
26	6.38	2.00	0.390	0.246	1.70	5.60	6.92	1.40	0.130	0.220	0.032	0.047
27	6.74	2.73	0.430	0.272	2.00	4.58	6.92	1.60	0.130	0.220	0.026	0.041
28	7.82	4.46	0.470	0.298	1.90	3.86	7.28	1.60	0.130	0.202	0.023	0.029
29	8.80	6.20	0.550	0.272	-----	3.62	7.64	1.15	0.117	0.220	0.023	0.020
30	8.80	6.56	0.635	0.298	-----	3.74	7.28	0.975	1.80	0.805	0.018	0.026
31	12.6	-----	0.720	0.298	-----	5.15	-----	0.805	-----	0.430	0.018	-----
Maks.	14.9	10.9	5.30	0.890	2.40	6.38	10.0	9.40	6.74	1.80	0.272	0.470
Min.	0.390	1.06	0.298	0.202	0.298	1.50	4.70	0.805	0.090	0.117	0.018	0.014
Ortalama	6.13	3.96	1.69	0.413	0.895	2.99	6.86	4.30	0.298	0.491	0.054	0.036
LT/SN/Km2	36.3	23.4	10.0	2.44	5.29	17.7	40.6	25.5	1.76	2.90	0.317	0.210
AKIM mm.	97.2	60.7	26.9	6.54	12.8	47.4	105.	68.2	4.57	7.78	0.849	0.545
MİL. M3	16.4	10.3	4.54	1.11	2.16	8.01	17.8	11.5	0.772	1.31	0.144	0.092

SU YILI (2006) YILLIK TOPLAM AKIM 74.14 MİLYON M3 439 MM. 13.9 LT/SN/Km2

22. Dogu Karadeniz Havzasi

D22A101 ALTIN D. BAKIRCILAR

YERİ : **MAÇKA SÜMELA YOLU ÜZERİ SOL SAHİLDEDİR.**
39°36'56" Doğu - 40°47'51" Kuzey

YAĞIŞ ALANI : **261,00 km2** **YAKLAŞIK KOT : 450 m**

GÖZLEM SÜRESİ : **01.10.2004 - 30.09.2006**

ORTALAMA AKIMLAR : **Gözlem süresinde 6.213 m3/sn. (2 Yıllık) 2006 Su yılında 6.824 m3/sn.**

ANLIK EN ÇOK VE EN AZ AKIMLAR:

2006 Su yılında anlık ençok akım	**:**	**59.7**	**m3/sn**	**31.10.2005**
2006 Su yılında anlık enaz akım	**:**	**0.988**	**m3/sn**	**20.09.2006**
Gözlem süresinde anlık ençok akım	**:**	**59.7**	**m3/sn**	**31.10.2005**
Gözlem süresinde anlık enaz akım	**:**	**0.988**	**m3/sn**	**20.09.2006**

Akımlar 01 Ekim 2005 'den 30 Eylül 2006' a kadar m3/sn olarak

Gün	Ekim	Kasım	Aralık	Ocak	Şubat	Mart	Nisan	Mayıs	Haziran	Temmuz	Ağustos	Eylül
01	1.63	36.9	7.11	2.11	1.63	4.17	5.31	25.7	15.6	4.74	2.98	1.25
02	1.55	26.3	5.73	2.35	1.63	3.98	8.70	23.1	14.4	5.73	2.85	1.25
03	1.35	16.8	5.73	2.35	1.63	4.17	7.80	25.2	13.4	8.40	2.60	1.35
04	3.48	13.7	6.65	2.27	1.71	3.98	8.40	31.6	12.7	8.70	2.35	1.35
05	9.30	11.1	6.19	2.27	1.71	4.55	9.30	26.3	12.1	8.10	2.19	1.55
06	6.65	10.2	5.50	2.27	1.71	3.48	8.10	26.8	11.8	7.11	2.03	1.55
07	3.48	9.30	4.93	2.85	1.79	3.23	6.88	30.5	11.8	7.34	1.95	1.35
08	2.73	9.00	4.36	3.10	2.19	3.48	6.65	31.1	12.1	8.70	1.87	1.40
09	2.27	11.4	3.98	3.10	2.11	5.50	9.00	30.0	11.4	15.6	1.79	1.35
10	1.95	9.90	3.60	2.73	2.35	8.70	17.2	28.9	10.2	10.5	1.87	1.30
11	1.79	8.40	3.35	2.35	2.19	5.50	18.8	27.3	9.00	7.11	1.79	1.25
12	1.63	7.34	3.23	2.27	2.27	4.17	18.8	23.1	8.10	5.73	1.71	1.25
13	1.55	6.42	3.23	2.11	2.60	3.60	18.8	21.2	9.00	4.93	1.55	2.03
14	1.50	5.50	2.85	2.11	2.48	3.35	18.4	23.1	7.34	4.55	1.55	1.79
15	1.55	5.12	2.60	2.03	2.19	3.23	19.6	27.3	6.88	4.17	1.55	1.45
16	2.98	4.74	2.60	1.95	2.11	4.36	23.1	25.7	6.65	4.17	1.50	1.40
17	2.35	4.55	2.60	1.79	2.03	3.98	22.5	22.0	6.19	3.60	1.55	1.35
18	7.80	3.98	2.48	1.79	1.87	3.48	18.8	22.0	7.34	3.23	1.45	1.30
19	9.60	3.60	2.35	1.79	2.03	3.23	20.4	22.0	6.88	3.23	1.50	1.25
20	13.0	3.60	2.35	1.79	2.85	3.10	16.8	18.8	6.42	3.98	1.55	1.20
21	13.0	3.48	2.48	1.79	3.35	2.98	15.2	17.6	5.96	4.93	1.50	1.15
22	8.40	3.48	2.35	1.71	3.10	2.85	17.2	17.6	5.50	5.96	1.45	1.15
23	6.88	3.60	2.27	1.79	3.10	2.85	20.8	17.2	4.93	5.31	1.40	1.25
24	6.19	3.23	2.35	1.79	3.23	2.98	19.6	17.6	4.74	4.55	1.35	1.45
25	5.31	3.23	2.35	1.71	3.23	4.55	20.8	17.2	4.55	4.36	1.40	1.35
26	4.74	3.23	2.35	1.71	3.60	7.11	33.7	17.6	4.36	4.55	1.35	1.25
27	6.42	3.48	2.27	1.71	4.36	6.19	32.1	17.6	4.17	4.17	1.30	1.35
28	5.50	3.79	2.19	1.71	4.36	4.55	23.1	19.2	4.17	3.79	1.30	1.30
29	5.73	4.74	2.19	1.71	-----	4.17	18.0	18.0	4.74	3.79	1.30	1.25
30	6.65	4.93	2.19	1.63	-----	3.98	16.0	15.2	5.96	3.48	1.30	1.20
31	7.34	-----	2.19	1.63	-----	4.17	-----	15.2	-----	3.35	1.25	-----
Maks.	59.7	36.9	7.34	3.79	4.55	10.5	38.7	35.3	16.0	21.2	2.98	3.10
Min.	1.15	2.85	2.03	1.55	1.55	2.73	5.12	13.4	4.17	2.85	1.20	0.988
Ortalama	4.98	8.17	3.44	2.07	2.48	4.18	16.7	22.6	8.28	5.74	1.71	1.36
LT/SN/Km2	19.1	31.3	13.2	7.94	9.50	16.0	63.8	86.7	31.7	22.0	6.56	5.19
AKIM mm.	51.1	81.1	35.3	21.3	23.0	42.9	165.	232.	82.2	58.9	17.6	13.5
MİL. M3	13.3	21.2	9.21	5.55	6.00	11.2	43.2	60.6	21.5	15.4	4.59	3.51

SU YILI (2006) YILLIK TOPLAM AKIM 215.26 MİLYON M3 825 MM. 26.1 LT/SN/Km2

22. Dogu Karadeniz Havzasi

D22A105 DEĞİRMEN D. SALIPAZARI

YERİ : SALIPAZARI İLÇESİNİN 15 KM GÜNEYİNDEKİ KAYAKÖPRÜ MAH. KÖPRÜSÜNDEDİR. 25 LİK PAFTADAKİ YERİ: F37-C4
36°49'19" Doğu - 41°4'24" Kuzey

YAĞIŞ ALANI : 74,50 km2 YAKLAŞIK KOT : 75 m

GÖZLEM SÜRESİ : 14.10.2003 - 30.09.2006

ORTALAMA AKIMLAR : Gözlem süresinde 2.945 m3/sn. (3 Yıllık) 2006 Su yılında 3.702 m3/sn.

ANLIK EN ÇOK VE EN AZ AKIMLAR:

2006 Su yılında anlık ençok akım	:	170.	m3/sn	30.06.2006
2006 Su yılında anlık enaz akım	:	0.090	m3/sn	04.08.2006
Gözlem süresinde anlık ençok akım	:	170.	m3/sn	30.06.2006
Gözlem süresinde anlık enaz akım	:	0.090	m3/sn	15.08.2005

1. Anahtar Eğrisi (Seviyeler cm olarak)

Seviye	Akım	Seviye	Akım	Seviye	Akım	Seviye	Akım
64	0.011	76	0.190	95	1.7	180	43.0
68	0.024	78	0.260	106	3.8	200	60.0
70	0.052	82	0.420	120	8.2	220	78.0
72	0.090	85	0.600	140	17.0	300	170.
74	0.138	89	0.940	160	28.5	400	340.

Akımlar 01 Ekim 2005 'den 30 Eylül 2006' a kadar m3/sn olarak

Gün	Ekim	Kasım	Aralık	Ocak	Şubat	Mart	Nisan	Mayıs	Haziran	Temmuz	Ağustos	Eylül
01	0.375	0.480	1.00	3.00	1.28	6.50	1.28	1.00	0.420	69.0	35.0	4.05
02	0.260	0.375	0.895	2.42	1.28	4.80	4.80	1.70	0.330	43.0	28.5	2.80
03	0.940	0.375	0.850	2.06	1.70	4.80	7.52	2.24	0.260	28.5	4.80	1.56
04	0.940	0.375	0.725	1.56	2.42	5.48	3.60	1.56	0.190	17.0	0.090	1.56
05	1.00	3.60	0.600	1.14	2.80	2.80	2.80	1.42	0.190	4.80	0.110	1.56
06	0.480	6.50	0.540	1.28	3.80	2.42	2.06	1.28	0.190	2.60	0.138	1.56
07	0.600	9.04	0.480	2.60	6.50	2.60	1.42	1.42	0.138	2.24	0.190	1.42
08	0.420	22.5	0.420	9.04	3.60	2.42	1.28	3.20	0.160	1.88	0.260	1.42
09	0.330	7.52	0.540	4.30	4.05	2.24	1.00	2.80	0.220	1.56	0.260	1.42
10	0.260	3.20	0.725	2.80	4.05	1.70	1.56	2.24	1.28	1.28	0.330	1.28
11	0.260	1.88	1.28	2.80	11.6	1.56	1.88	1.14	1.00	1.00	0.330	1.28
12	0.480	1.14	2.80	3.20	6.50	1.42	1.42	0.940	0.895	1.00	0.330	1.28
13	1.42	0.895	1.70	3.60	3.80	1.28	1.14	1.14	0.725	0.895	0.480	1.28
14	2.24	0.725	1.14	3.20	3.00	1.14	0.940	5.48	0.540	0.895	0.540	1.00
15	2.42	0.600	0.940	2.42	2.60	1.14	0.940	3.00	0.420	0.725	0.540	0.895
16	6.84	0.600	0.850	1.88	2.42	1.28	1.42	1.70	0.420	0.600	0.600	0.725
17	14.7	0.480	0.600	1.56	2.24	2.06	1.14	2.24	0.420	0.600	0.600	0.895
18	3.80	0.480	0.480	1.42	8.62	2.42	0.940	3.00	0.330	0.600	0.725	1.00
19	4.55	0.420	0.540	1.14	14.2	9.04	0.850	2.60	0.330	0.600	0.725	1.00
20	6.50	0.330	3.20	3.40	12.4	6.84	0.725	1.56	0.260	0.600	0.850	0.895
21	5.14	13.3	1.56	2.42	10.3	5.48	0.600	1.00	0.260	0.725	0.895	0.940
22	3.00	11.1	0.940	2.06	8.20	4.80	0.600	0.895	0.190	0.725	0.850	1.00
23	1.42	4.05	0.895	2.24	7.86	3.40	0.540	0.540	0.160	0.725	0.725	0.940
24	0.850	3.00	0.895	1.70	7.52	2.42	6.50	0.480	0.160	0.540	0.725	0.895
25	0.725	4.55	1.00	1.42	10.3	5.82	12.4	0.420	0.160	0.540	0.725	0.895
26	0.725	8.20	1.00	1.56	9.46	5.48	5.14	0.375	0.160	0.540	0.725	4.80
27	0.480	4.30	1.00	1.42	8.20	3.80	3.20	1.42	0.540	0.540	0.725	2.60
28	0.540	2.42	1.56	1.28	6.50	3.40	2.24	1.42	6.84	0.540	0.725	1.70
29	0.725	1.42	2.60	1.28	-----	2.60	1.70	0.725	6.50	43.0	0.375	1.28
30	0.540	1.42	2.24	1.28	-----	1.88	1.28	0.480	170.	69.0	0.420	1.14
31	0.540	-----	2.42	1.14	-----	1.56	-----	0.480	-----	51.0	0.540	-----
Maks.	28.5	33.1	4.05	11.1	18.7	15.2	22.0	7.52	170.	110.	35.0	8.62
Min.	0.220	0.220	0.420	1.00	1.14	1.00	0.540	0.375	0.110	0.540	0.090	0.600
Ortalama	2.05	3.84	1.17	2.34	5.97	3.37	2.43	1.61	6.46	11.2	2.67	1.50
LT/SN/Km2	27.5	51.6	15.8	31.4	80.2	45.3	32.6	21.6	86.7	150.	35.9	20.2
AKIM mm.	73.6	134.	42.2	84.2	194.	121.	84.6	57.9	225.	403.	96.1	52.3
MİL. M3	5.49	9.96	3.15	6.27	14.4	9.04	6.30	4.31	16.7	30.0	7.16	3.89

SU YILI (2006) YILLIK TOPLAM AKIM 116.67 MİLYON M3 1566 MM. 49.7 LT/SN/Km2

22. Dogu Karadeniz Havzasi

D22A106 BATLAMA D. ÇUKURKÖY

YERİ : **GİRESUN BATLAMA YOLU ÜZERİNDE 10.KM DERENİN SAĞ SAHİLİNDE YAYA KÖPRÜSÜNÜN AYAĞINDADIR**

38°18'34" Doğu - 40°50'44" Kuzey

YAĞIŞ ALANI : **122,00 km2** **YAKLAŞIK KOT : 600 m**

GÖZLEM SÜRESİ : **01.10.2004 - 30.09.2006**

ORTALAMA AKIMLAR : **Gözlem süresinde 3.684 m3/sn. (2 Yıllık) 2006 Su yılında 3.242 m3/sn.**

ANLIK EN ÇOK VE EN AZ AKIMLAR:

2006 Su yılında anlık ençok akım	:	**107.**	**m3/sn**	**03.07.2006**
2006 Su yılında anlık enaz akım	:	**0.638**	**m3/sn**	**30.09.2006**
Gözlem süresinde anlık ençok akım	:	**107.**	**m3/sn**	**03.07.2006**
Gözlem süresinde anlık enaz akım	:	**0.536**	**m3/sn**	**14.06.2005**

Akımlar 01 Ekim 2005 'den 30 Eylül 2006' a kadar m3/sn olarak

Gün	Ekim	Kasım	Aralık	Ocak	Şubat	Mart	Nisan	Mayıs	Haziran	Temmuz	Ağustos	Eylül
01	2.34	13.0	4.20	2.34	1.30	8.84	2.34	2.18	1.03	0.842	1.50	0.842
02	1.40	9.88	3.02	3.54	1.30	5.00	2.50	2.34	1.08	1.50	1.14	0.842
03	1.70	6.60	2.18	2.50	1.40	8.84	5.40	6.20	1.03	37.2	1.14	1.03
04	4.60	5.00	1.86	2.18	1.50	5.40	11.4	8.84	0.968	22.6	1.14	1.03
05	20.7	3.80	1.86	1.86	1.86	7.80	7.80	4.60	1.03	7.40	1.08	1.08
06	7.80	8.32	1.60	1.86	1.86	5.00	5.00	4.20	0.968	3.80	1.08	0.968
07	3.02	10.4	1.50	3.02	2.02	5.00	3.28	6.20	1.03	2.76	1.08	0.910
08	2.34	10.4	1.40	3.28	4.60	4.20	3.02	10.9	0.968	2.50	1.03	1.03
09	1.70	16.5	1.50	6.20	2.50	7.40	4.20	12.0	1.03	3.02	0.910	0.910
10	1.50	12.0	1.60	3.54	2.76	6.60	5.00	8.32	0.968	2.18	0.968	0.910
11	1.40	7.40	1.60	2.34	2.34	7.40	3.80	6.20	1.03	2.34	0.968	0.910
12	1.30	5.40	1.50	1.86	5.00	2.50	5.00	4.60	1.03	2.02	0.968	0.842
13	1.40	3.80	1.40	1.60	4.60	2.34	3.80	2.76	0.968	2.02	0.968	1.30
14	1.50	2.76	1.40	1.50	3.02	2.34	3.28	2.50	0.968	2.02	0.968	1.30
15	1.60	2.18	1.20	1.40	2.50	3.02	5.80	2.76	0.968	1.86	0.968	1.03
16	1.40	2.02	1.30	1.30	2.18	7.40	2.18	2.76	0.968	1.70	0.910	1.03
17	2.34	1.86	1.30	1.20	2.02	4.60	2.18	2.50	0.968	1.50	0.910	0.968
18	20.0	1.40	1.30	1.14	4.20	3.28	1.60	2.50	0.910	1.50	0.910	0.842
19	25.9	1.50	1.40	1.08	2.76	3.02	2.76	2.50	0.910	1.50	0.910	0.842
20	25.2	1.50	1.50	1.03	10.9	2.76	2.50	2.34	0.910	1.50	0.910	0.842
21	15.1	2.50	1.86	1.40	7.80	3.54	2.34	2.02	0.910	1.50	0.910	0.842
22	10.4	7.00	1.30	1.20	5.80	3.02	2.34	1.60	0.910	1.50	0.968	0.842
23	7.00	4.60	1.20	1.20	4.60	2.50	2.18	1.50	0.910	1.50	0.910	0.910
24	5.00	3.28	1.60	1.40	4.20	2.50	2.76	1.20	0.842	1.50	0.910	1.03
25	3.54	3.54	1.70	1.40	3.80	4.60	6.60	1.14	0.842	1.50	0.910	1.03
26	3.28	7.00	2.18	1.30	5.40	5.80	13.7	1.08	0.842	1.40	0.910	0.910
27	5.00	5.80	2.02	1.30	3.02	3.54	5.40	1.08	0.842	1.30	0.910	0.910
28	3.28	5.40	1.86	1.30	7.00	2.76	2.76	1.03	0.842	1.30	0.910	0.842
29	7.80	4.60	2.18	1.30	-----	2.50	2.18	1.03	0.842	1.30	0.910	0.842
30	13.7	3.02	2.76	1.40	-----	1.86	2.18	1.14	0.842	1.30	0.910	0.774
31	11.4	-----	3.02	1.50	-----	1.86	-----	1.03	-----	1.50	0.842	-----
Maks.	39.7	18.6	5.40	7.80	17.9	16.5	29.8	20.0	1.50	107.	1.50	1.70
Min.	1.30	1.40	1.20	1.03	1.14	1.86	1.60	1.03	0.842	0.774	0.842	0.638
Ortalama	6.92	5.75	1.82	1.92	3.65	4.43	4.18	3.58	0.945	3.79	0.983	0.946
LT/SN/Km2	56.8	47.1	14.9	15.7	29.9	36.3	34.2	29.4	7.75	31.0	8.05	7.76
AKIM mm.	152.	122.	39.9	42.1	72.4	97.2	88.7	78.6	20.1	83.1	21.6	20.1
MİL. M3	18.5	14.9	4.86	5.14	8.83	11.9	10.8	9.59	2.45	10.1	2.63	2.45

SU YILI (2006) YILLIK TOPLAM AKIM 102.15 MİLYON M3 837 MM. 26.6 LT/SN/Km2

22. Dogu Karadeniz Havzasi

D22A107 Sögütlü D. Düzköy

YERİ : **TRABZON DÜZKÖY YOLUNUN ÜZERİNDE DERENİN SAĞ SAHİLİNDE.**
39°28'10" Doğu - 40°54'10" Kuzey

YAĞIŞ ALANI : **129,00 km2** **YAKLAŞIK KOT : 410 m**

GÖZLEM SÜRESİ : **01.10.2004 - 30.09.2006**

ORTALAMA AKIMLAR : **Gözlem süresinde 3.714 m3/sn. (2 Yıllık) 2006 Su yılında 4.816 m3/sn.**

ANLIK EN ÇOK VE EN AZ AKIMLAR:

2006 Su yılında anlık ençok akım	:	**94.4**	**m3/sn**	**20.10.2005**
2006 Su yılında anlık enaz akım	:	**0.330**	**m3/sn**	**29.01.2006**
Gözlem süresinde anlık ençok akım	:	**94.4**	**m3/sn**	**20.10.2005**
Gözlem süresinde anlık enaz akım	:	**0.233**	**m3/sn**	**25.09.2005**

Akımlar 01 Ekim 2005 'den 30 Eylül 2006' a kadar m3/sn olarak

Gün	Ekim	Kasım	Aralık	Ocak	Şubat	Mart	Nisan	Mayıs	Haziran	Temmuz	Ağustos	Eylül
01	1.23	39.7	15.2	1.40	0.408	5.92	6.70	8.00	1.32	12.4	2.20	1.22
02	0.928	27.3	12.8	1.32	0.408	6.44	6.70	8.00	1.32	7.74	2.20	1.22
03	0.694	10.7	10.0	1.23	0.408	6.18	9.36	12.8	1.15	20.9	1.88	0.510
04	0.668	10.4	11.4	1.15	0.421	7.22	11.4	14.8	1.06	17.8	1.72	0.524
05	5.40	6.18	10.4	1.06	0.512	7.22	20.9	12.8	0.980	6.18	1.40	0.648
06	19.0	5.16	7.74	0.980	0.564	4.68	12.8	9.36	0.928	3.96	1.32	0.682
07	5.66	5.66	6.44	0.928	0.616	4.68	9.02	12.1	0.876	6.44	1.06	0.580
08	4.44	7.74	5.16	0.980	1.15	4.68	6.96	8.34	0.876	6.70	0.928	0.580
09	4.92	28.9	5.40	0.928	1.23	13.1	5.92	22.4	0.980	8.34	0.928	0.682
10	6.44	14.5	5.40	0.876	3.48	12.4	6.70	19.4	0.980	4.68	0.980	0.580
11	7.48	5.16	4.44	0.772	1.32	5.92	9.02	14.8	0.928	2.84	0.980	0.552
12	7.74	5.16	4.20	0.642	3.48	3.00	7.48	8.00	0.928	2.36	0.980	0.900
13	8.00	4.92	4.20	0.564	3.00	2.52	6.44	5.40	1.23	1.88	0.980	1.22
14	8.34	4.20	3.00	0.512	1.40	2.04	5.40	4.92	1.88	1.40	0.980	2.36
15	8.34	3.24	2.84	0.486	0.928	5.66	4.92	7.74	1.15	1.32	0.980	0.876
16	8.00	2.68	2.68	0.460	0.772	10.7	4.44	6.44	2.36	1.15	0.980	0.668
17	8.00	2.20	3.72	0.447	0.668	9.02	4.20	4.44	5.16	1.06	0.980	0.642
18	26.6	2.04	4.20	0.447	0.590	7.22	4.68	3.48	4.68	1.23	0.980	0.590
19	31.4	2.04	5.92	0.434	0.824	5.92	2.68	2.68	14.8	2.52	0.980	0.564
20	53.0	1.72	8.00	0.421	11.4	5.16	2.20	2.20	11.4	3.72	0.980	0.564
21	19.0	1.40	10.7	0.408	5.92	4.44	1.88	1.88	8.00	3.72	0.980	0.590
22	7.22	1.72	6.70	0.408	3.96	3.96	1.72	1.56	6.96	2.52	2.20	0.824
23	4.68	1.56	3.24	0.408	4.20	3.24	2.20	1.32	6.44	2.20	2.28	0.772
24	6.44	1.56	3.96	0.421	4.68	3.48	2.20	1.15	5.16	2.68	2.00	0.824
25	7.74	1.56	2.04	0.408	4.68	3.96	4.20	1.06	5.40	2.84	1.60	0.928
26	8.34	1.72	2.04	0.408	7.74	7.74	13.4	1.15	4.92	2.52	1.50	2.52
27	5.16	2.68	2.04	0.408	10.4	9.36	23.5	1.15	4.92	2.36	1.50	0.876
28	7.22	7.22	1.88	0.395	8.34	7.74	9.36	2.36	5.40	2.36	1.43	0.928
29	12.4	9.36	1.72	0.395	-----	6.18	6.18	1.72	5.92	2.20	1.43	0.928
30	9.02	11.7	1.88	0.382	-----	5.66	5.40	1.40	8.34	2.20	1.29	0.772
31	8.68	-----	1.88	0.408	-----	5.40	-----	1.56	-----	2.68	1.22	-----
Maks.	94.4	47.0	16.7	1.40	15.6	14.8	34.1	30.5	23.2	41.0	8.68	10.4
Min.	0.402	1.15	0.980	0.330	0.369	2.04	1.56	0.824	0.876	0.928	0.512	0.510
Ortalama	10.1	7.67	5.52	0.661	2.98	6.16	7.27	6.59	3.88	4.61	1.35	0.871
LT/SN/Km2	78.1	59.5	42.8	5.12	23.1	47.7	56.3	51.1	30.1	35.7	10.5	6.75
AKIM mm.	209.	154.	115.	13.7	55.9	128.	146.	137.	78.0	95.7	28.0	17.5
MİL. M3	27.0	19.9	14.8	1.77	7.21	16.5	18.8	17.7	10.1	12.3	3.62	2.26

SU YILI (2006) YILLIK TOPLAM AKIM 151.96 MİLYON M3 1178 MM. 37.3 LT/SN/Km2

22. Dogu Karadeniz Havzasi

D22A108 Hemsin D. Basköy

YERİ : **RİZE-PAZAR-HEMŞİN YOLUNUN ÜZERİNDE 20. KM DE DERENİN SAĞ SAHİLİNDE, YAYA KÖPRÜSÜNÜN AYAĞINDA.**
40°53'20" Doğu - 41°5'1" Kuzey

YAĞIŞ ALANI : **139,00 km2** **YAKLAŞIK KOT : 175 m**

GÖZLEM SÜRESİ : **01.10.2004 - 30.09.2006**

ORTALAMA AKIMLAR : **Gözlem süresinde 5.263 m3/sn. (1 Yıllık) 2006 Su yılında 5.263 m3/sn.**

ANLIK EN ÇOK VE EN AZ AKIMLAR:

2006 Su yılında anlık ençok akım	:	**61.2**	**m3/sn**	**04.10.2005**
2006 Su yılında anlık enaz akım	:	**0.437**	**m3/sn**	**25.09.2006**
Gözlem süresinde anlık ençok akım	:	**61.2**	**m3/sn**	**04.10.2005**
Gözlem süresinde anlık enaz akım	:	**0.437**	**m3/sn**	**25.09.2006**

Akımlar 01 Ekim 2005 'den 30 Eylül 2006' a kadar m3/sn olarak

Gün	Ekim	Kasım	Aralık	Ocak	Şubat	Mart	Nisan	Mayıs	Haziran	Temmuz	Ağustos	Eylül
01	16.2	15.3	9.44	2.90	2.40	5.06	2.70	7.20	2.40	24.0	2.70	0.724
02	14.0	16.6	7.52	3.30	2.40	7.19	2.34	7.84	2.40	17.9	2.40	0.900
03	13.6	13.6	6.70	3.30	2.40	5.98	2.34	10.1	2.40	27.5	2.09	2.09
04	38.0	12.9	8.16	3.10	2.24	6.21	2.09	8.16	2.40	26.5	1.94	3.90
05	33.5	11.5	7.52	2.90	2.40	4.07	1.85	6.95	2.40	14.4	1.68	2.70
06	23.5	12.2	6.70	3.10	2.55	4.42	1.85	6.20	2.40	12.2	1.56	5.45
07	12.2	14.4	5.95	4.95	2.70	4.60	1.73	5.70	2.40	11.5	1.43	5.06
08	9.76	12.9	5.70	4.30	3.70	6.21	2.34	6.20	2.40	16.6	1.30	1.44
09	8.16	27.0	5.20	4.30	4.30	6.90	3.00	5.95	2.40	9.44	1.56	0.863
10	7.20	23.5	4.70	4.10	4.95	4.24	2.46	5.20	2.55	6.95	1.30	0.621
11	6.70	17.4	4.70	3.50	4.70	2.82	2.34	4.70	3.30	5.45	1.30	0.515
12	6.20	15.3	4.50	3.50	6.70	2.58	2.09	4.30	4.70	4.50	1.20	1.36
13	5.70	17.4	4.50	3.30	2.82	2.58	2.09	4.30	3.30	3.90	1.20	1.73
14	5.70	14.4	4.10	2.90	2.70	2.70	1.85	7.84	2.40	3.50	1.20	1.03
15	7.84	12.9	3.90	2.90	2.34	3.18	1.85	5.95	2.40	4.95	1.20	2.82
16	7.52	11.5	3.70	2.90	2.22	2.70	1.97	4.70	2.40	3.50	1.10	4.07
17	11.8	10.8	3.90	2.70	2.22	2.34	1.44	4.70	3.90	3.10	1.10	1.44
18	9.44	10.4	3.90	2.55	1.73	2.09	1.28	4.30	5.45	2.90	1.56	0.946
19	23.5	8.80	3.70	2.40	1.73	2.22	1.11	3.90	3.90	4.10	2.09	0.674
20	26.0	8.48	3.70	2.40	2.58	2.22	1.28	3.50	2.90	5.20	1.30	0.515
21	20.0	8.16	3.70	2.90	2.34	1.97	1.44	3.30	2.55	4.70	1.30	0.515
22	16.6	7.52	3.70	2.40	2.22	2.09	1.28	3.10	2.40	4.30	1.10	1.03
23	14.0	7.20	3.30	3.10	2.70	2.22	1.28	2.90	2.40	3.50	1.00	0.780
24	12.9	6.95	3.30	2.90	3.35	3.71	2.82	2.90	2.40	3.30	0.900	0.515
25	12.6	6.70	3.30	2.70	4.24	3.18	5.29	2.90	2.55	3.30	0.900	0.437
26	13.6	6.45	3.30	2.70	5.52	2.58	6.70	2.70	3.30	2.90	0.900	3.89
27	12.6	6.20	3.30	2.70	5.52	1.97	5.20	3.10	4.70	2.70	0.800	3.71
28	19.1	6.20	3.30	2.70	4.42	1.85	4.70	3.70	4.50	3.30	0.800	1.61
29	21.2	6.45	2.90	2.55	-----	1.73	4.50	2.90	3.70	4.30	0.800	1.11
30	16.6	7.84	2.90	2.40	-----	1.85	9.76	2.55	3.90	4.30	1.20	0.863
31	17.0	-----	2.90	2.24	-----	2.09	-----	2.40	-----	3.10	0.800	-----
Maks.	61.2	32.4	10.4	5.95	6.70	12.1	9.76	14.0	8.16	42.5	20.8	34.6
Min.	5.70	6.20	2.70	2.24	1.73	1.53	1.03	2.40	2.40	2.55	0.724	0.437
Ortalama	14.9	11.9	4.65	3.05	3.22	3.40	2.77	4.84	3.04	7.99	1.35	1.78
LT/SN/Km2	107.	85.6	33.4	22.0	23.1	24.5	19.9	34.8	21.9	57.5	9.68	12.8
AKIM mm.	288.	222.	89.6	58.8	56.0	65.6	51.6	93.3	56.7	154.	25.9	33.1
MİL. M3	40.0	30.8	12.4	8.17	7.78	9.12	7.17	13.0	7.88	21.4	3.60	4.61

SU YILI (2006) YILLIK TOPLAM AKIM 165.93 MİLYON M3 1194 MM. 37.9 LT/SN/Km2

23

ÇORUH HAVZASI

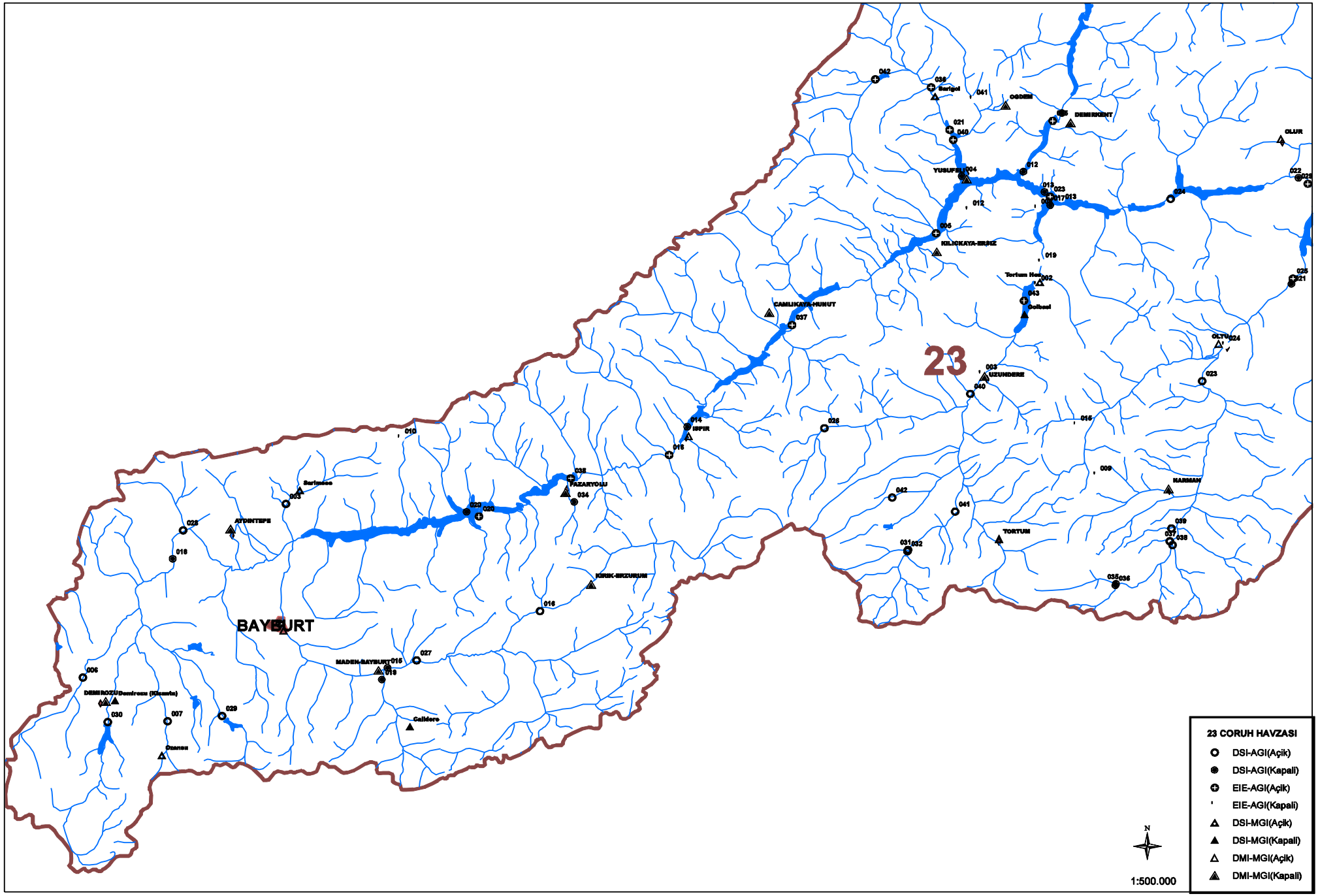
23
BAYBURT
YUSUFELI
KILICKAYA-ERSIZ
CAMLIKAYA-HUNUT
OGDEM
DEMIRKENT
OLUR
Tortum Hes
Dolbent
UZUNDERE
GLTU
HARMAN
TORTUM
IPPIR
FAZARYOLU
KIRIK-ERZURUM
AYDINTEPE
Sarimese
MADEN-BAYBURT
Caldere
DEMIROZU
Demiroz (Kizanlu)
Demiroz
23 CORUH HAVZASI
DSI-AGI(Açik)
DSI-AGI(Kapali)
EIE-AGI(Açik)
EIE-AGI(Kapali)
DSI-MGI(Açik)
DSI-MGI(Kapali)
DMI-MGI(Açik)
DMI-MGI(Kapali)
N
1:500.000

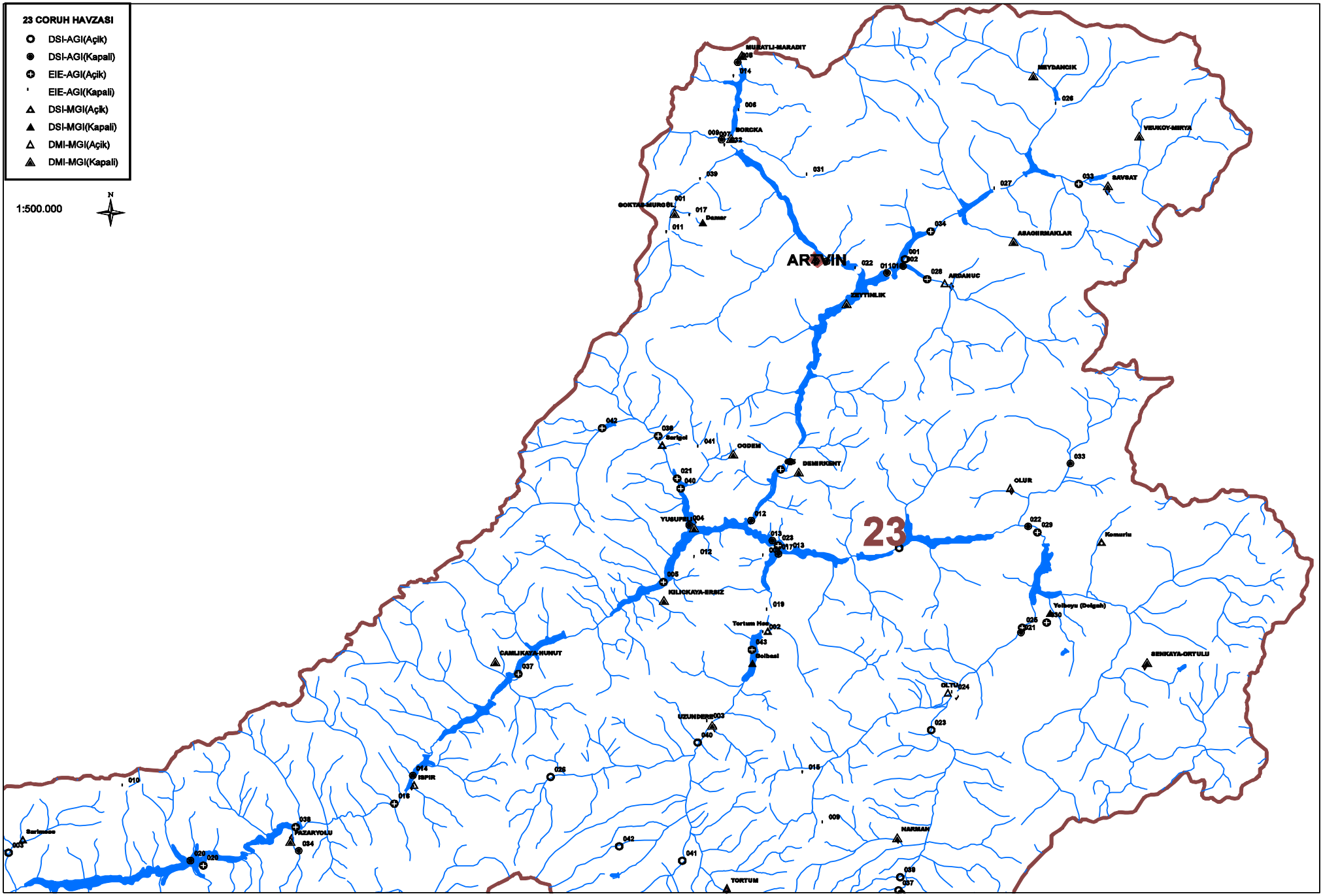
23 CORUH HAVZASI
DSI-AGI(Açik)
DSI-AGI(Kapali)
EIE-AGI(Açik)
EIE-AGI(Kapali)
DSI-MGI(Açik)
DSI-MGI(Kapali)
DMI-MGI(Açik)
DMI-MGI(Kapali)
1:500.000
N
ARTVIN
23
MURATLI-MARADIT
MEYDANCIK
VISUKOY-MIKYA
BORCKA
SAVSAT
GOKTAS-MURGUL
Damar
ASAGIRMAKLAR
ARDANUC
ZEYTINLIK
Sarigol
OGDEM
DEMIRKENT
OLUR
YUSUFELI
Komurlu
KILICKAYA-ERSIZ
Yeltoyu (Dolgah)
Tortum Hes
Selbasi
SENKAYA-ORTULU
CAMLIKAYA-HUNUT
OLTU
UZUNDERE
INPIR
Sarisasa
HAZARYOLU
HARMAN
TORTUM

23. Çoruh Havzasi

D23A001 BERTA S. BERTA

YERİ : **ARTVİN ŞAVŞAT YOLU ÜZERINDE ARDANUÇ YOL AYRIMINDAN 1KM EMBADADIR.**
38°51'9" Doğu - 40°47'15" Kuzey

YAĞIŞ ALANI : **1680,00 km2** **YAKLAŞIK KOT : 310 m**

GÖZLEM SÜRESİ : **01.10.1961 - 28.02.2006**

ORTALAMA AKIMLAR : **Gözlem süresinde 26.969 m3/sn. (29 Yıllık) 2006 Su yılında ---- m3/sn.**

ANLIK EN ÇOK VE EN AZ AKIMLAR:

2006 Su yılında anlık ençok akım	:	----- m3/sn		
2006 Su yılında anlık enaz akım	:	----- m3/sn		
Gözlem süresinde anlık ençok akım	:	376.	m3/sn	11.05.1992
Gözlem süresinde anlık enaz akım	:	1.00	m3/sn	13.08.1970

Akımlar 01 Ekim 2005 'den 30 Eylül 2006' a kadar m3/sn olarak

Gün	Ekim	Kasım	Aralık	Ocak	Şubat	Mart	Nisan	Mayıs	Haziran	Temmuz	Ağustos	Eylül
01	11.2	71.6	32.3	15.2	12.2	-----	-----	-----	-----	-----	-----	-----
02	11.7	69.2	33.2	14.7	11.7	-----	-----	-----	-----	-----	-----	-----
03	9.00	64.4	53.6	15.2	12.2	-----	-----	-----	-----	-----	-----	-----
04	21.2	53.6	72.8	13.2	12.2	-----	-----	-----	-----	-----	-----	-----
05	29.7	46.9	62.0	13.7	12.7	-----	-----	-----	-----	-----	-----	-----
06	35.0	44.8	46.9	14.2	12.7	-----	-----	-----	-----	-----	-----	-----
07	30.5	40.6	39.5	14.7	13.2	-----	-----	-----	-----	-----	-----	-----
08	28.9	39.5	35.0	15.2	13.7	-----	-----	-----	-----	-----	-----	-----
09	24.1	39.5	30.5	15.7	16.2	-----	-----	-----	-----	-----	-----	-----
10	22.5	36.8	30.5	13.7	16.2	-----	-----	-----	-----	-----	-----	-----
11	21.2	32.3	29.7	13.7	15.2	-----	-----	-----	-----	-----	-----	-----
12	20.0	31.4	24.9	13.2	16.8	-----	-----	-----	-----	-----	-----	-----
13	21.2	31.4	22.5	12.7	18.1	-----	-----	-----	-----	-----	-----	-----
14	20.0	35.9	21.2	12.2	17.5	-----	-----	-----	-----	-----	-----	-----
15	20.0	35.0	20.6	13.2	16.8	-----	-----	-----	-----	-----	-----	-----
16	21.2	34.1	21.2	12.2	15.7	-----	-----	-----	-----	-----	-----	-----
17	22.5	30.5	21.2	11.7	13.2	-----	-----	-----	-----	-----	-----	-----
18	35.9	26.5	20.0	12.2	13.2	-----	-----	-----	-----	-----	-----	-----
19	37.7	28.9	19.4	11.2	14.2	-----	-----	-----	-----	-----	-----	-----
20	54.8	28.1	20.0	11.7	13.2	-----	-----	-----	-----	-----	-----	-----
21	57.2	28.1	19.4	12.2	13.2	-----	-----	-----	-----	-----	-----	-----
22	47.9	27.3	18.1	13.2	15.2	-----	-----	-----	-----	-----	-----	-----
23	42.7	28.9	16.8	12.7	16.2	-----	-----	-----	-----	-----	-----	-----
24	41.6	28.1	18.1	12.2	20.6	-----	-----	-----	-----	-----	-----	-----
25	41.6	24.9	17.5	13.2	21.2	-----	-----	-----	-----	-----	-----	-----
26	41.6	22.5	16.8	11.7	21.2	-----	-----	-----	-----	-----	-----	-----
27	60.8	22.5	15.7	12.7	24.9	-----	-----	-----	-----	-----	-----	-----
28	64.4	24.9	15.2	11.7	25.7	-----	-----	-----	-----	-----	-----	-----
29	81.0	30.5	12.2	11.7	-----	-----	-----	-----	-----	-----	-----	-----
30	71.6	34.1	13.7	12.2	-----	-----	-----	-----	-----	-----	-----	-----
31	71.6	-----	14.7	11.2	-----	-----	-----	-----	-----	-----	-----	-----
Maks.	83.8	71.6	74.0	15.7	25.7	--	--	--	--	--	--	--
Min.	8.20	22.5	11.7	11.2	11.7	--	--	--	--	--	--	--
Ortalama	36.1	36.4	26.9	13.0	15.9	--	--	--	--	--	--	--
LT/SN/Km2	21.5	21.7	16.0	7.76	9.46	--	--	--	--	--	--	--
AKIM mm.	57.6	56.2	43.0	20.8	22.9	--	--	--	--	--	--	--
MİL. M3	96.8	94.4	72.2	34.9	38.5	--	--	--	--	--	--	--

SU YILI (2006)

23. Çoruh Havzasi

D23A003 Çengül D. ERİKDIBI

YERİ : **BAYBURT-ÇAYKARA YOLUNUN 21. KM SİNDE ERİKDİBİ KÖYÜNDEDİR.**
40°15'0" Doğu - 40°25'45" Kuzey

YAĞIŞ ALANI : **162,02 km2** **YAKLAŞIK KOT : 1545 m**

GÖZLEM SÜRESİ : **01.10.1961 - 30.09.2006**

ORTALAMA AKIMLAR : **Gözlem süresinde 3.384 m3/sn. (41 Yıllık) 2006 Su yılında 2.262 m3/sn.**

ANLIK EN ÇOK VE EN AZ AKIMLAR:

2006 Su yılında anlık ençok akım	**:**	**26.5**	**m3/sn**	**15.03.2006**
2006 Su yılında anlık enaz akım	**:**	**0.025**	**m3/sn**	**27.02.2006**
Gözlem süresinde anlık ençok akım	**:**	**53.0**	**m3/sn**	**29.05.1979**
Gözlem süresinde anlık enaz akım	**:**	**0.001**	**m3/sn**	**31.08.1975**

Akımlar 01 Ekim 2005 'den 30 Eylül 2006' a kadar m3/sn olarak

Gün	Ekim	Kasım	Aralık	Ocak	Şubat	Mart	Nisan	Mayıs	Haziran	Temmuz	Ağustos	Eylül
01	0.484	4.18	0.935	0.435	0.435	0.228	3.92	6.80	7.40	0.435	0.366	0.025
02	0.484	3.14	0.935	0.435	0.435	0.935	4.18	10.2	7.10	0.297	0.366	0.038
03	0.620	2.62	0.935	0.435	0.435	1.43	4.18	14.6	6.80	0.228	0.297	0.038
04	1.00	2.10	1.10	0.435	0.435	1.10	3.66	12.6	6.50	0.366	0.366	0.038
05	0.812	2.10	1.10	0.435	0.435	1.10	2.88	11.2	5.90	0.297	0.297	0.038
06	0.716	2.10	1.10	0.435	0.366	1.43	2.62	10.9	5.60	0.297	0.090	0.038
07	0.716	1.93	1.10	0.435	0.159	1.93	2.62	12.2	5.90	0.228	0.064	0.051
08	0.716	1.77	0.935	0.435	0.159	2.36	3.14	18.5	5.00	0.435	0.051	0.051
09	0.716	1.43	0.935	0.435	0.159	3.66	5.30	20.5	4.18	0.435	0.038	0.038
10	0.620	1.10	0.768	0.435	0.159	2.88	6.20	16.5	3.66	0.297	0.064	0.051
11	0.620	1.10	0.768	0.435	0.159	2.10	7.10	13.6	3.14	0.297	0.077	0.064
12	0.552	1.10	0.768	0.435	0.159	1.93	6.80	11.7	3.14	0.228	0.064	0.077
13	0.552	0.935	0.602	0.435	0.159	1.93	6.80	11.2	2.88	0.090	0.038	0.090
14	0.552	0.768	0.602	0.435	0.159	25.0	6.50	10.5	2.36	0.064	0.051	0.077
15	0.812	0.768	0.602	0.435	0.090	26.5	6.80	9.10	2.10	0.064	0.038	0.090
16	0.716	0.768	0.768	0.435	0.077	9.45	7.40	9.45	2.10	0.038	0.051	0.159
17	1.55	0.602	0.768	0.435	0.077	0.935	7.40	9.80	1.93	0.228	0.051	0.228
18	1.10	0.602	0.602	0.435	0.077	0.602	6.80	8.75	1.77	0.602	0.051	0.159
19	2.19	0.602	0.768	0.435	0.077	0.435	6.20	7.70	1.43	1.10	0.064	0.090
20	2.02	0.435	0.768	0.435	0.077	0.435	6.50	8.05	1.27	0.602	0.077	0.064
21	1.70	0.768	0.602	0.435	0.077	0.366	7.10	8.75	1.10	0.602	0.297	0.038
22	1.55	0.602	0.602	0.435	0.077	0.366	7.10	9.45	0.935	0.602	0.159	0.051
23	1.40	0.435	0.602	0.435	0.077	0.435	6.80	9.45	0.768	0.602	0.090	0.077
24	1.40	0.435	0.435	0.435	0.077	0.935	8.40	9.45	0.935	0.435	0.051	0.159
25	1.40	0.435	0.435	0.435	0.077	1.93	8.05	9.10	0.768	0.366	0.038	0.228
26	1.55	0.435	0.435	0.435	0.077	2.10	7.10	9.10	0.768	0.366	0.051	0.297
27	1.55	0.435	0.435	0.435	0.038	2.10	5.60	9.10	0.768	0.297	0.077	0.366
28	1.55	0.602	0.435	0.435	0.038	2.10	5.30	8.75	0.602	0.366	0.159	0.366
29	1.70	0.768	0.435	0.435	-----	2.10	4.44	7.40	0.602	0.366	0.051	0.297
30	1.85	0.935	0.435	0.435	-----	2.62	6.20	6.80	0.602	0.366	0.025	0.159
31	3.20	-----	0.435	0.435	-----	3.14	-----	7.40	-----	0.366	0.025	-----
Maks.	3.20	5.00	1.10	0.435	0.435	26.5	8.40	25.0	7.40	1.10	0.768	0.366
Min.	0.484	0.435	0.366	0.435	0.025	0.228	2.62	6.80	0.602	0.025	0.025	0.025
Ortalama	1.17	1.20	0.714	0.435	0.172	3.37	5.77	10.6	2.93	0.367	0.116	0.118
LT/SN/Km2	7.25	7.41	4.41	2.68	1.06	20.8	35.6	65.4	18.1	2.26	0.714	0.729
AKIM mm.	19.4	19.2	11.8	7.19	2.57	55.8	92.3	175.	46.9	6.06	1.91	1.89
MİL. M3	3.14	3.11	1.91	1.17	0.417	9.03	15.0	28.4	7.60	0.982	0.310	0.306

SU YILI (2006) YILLIK TOPLAM AKIM 71.38 MİLYON M3 441 MM. 14.0 LT/SN/Km2

23. Çoruh Havzasi

D23A006 PULUR Ç. CİBRE

YERİ : **BAYBURTA 35 KM MESAFEDEKİ CİBRE KÖYÜ İÇİNDEDİR.**
39°51'41" Doğu - 40°12'10" Kuzey

YAĞIŞ ALANI : **186,81 km2** **YAKLAŞIK KOT : 1692 m**

GÖZLEM SÜRESİ : **11.11.1962 - 30.09.2006**

ORTALAMA AKIMLAR : **Gözlem süresinde 0.706 m3/sn. (39 Yıllık) 2006 Su yılında 1.332 m3/sn.**

ANLIK EN ÇOK VE EN AZ AKIMLAR:

2006 Su yılında anlık ençok akım	**:**	**8.96**	**m3/sn**	**08.05.2006**
2006 Su yılında anlık enaz akım	**:**	**0.155**	**m3/sn**	**11.11.2005**
Gözlem süresinde anlık ençok akım	**:**	**17.0**	**m3/sn**	**14.04.1988**
Gözlem süresinde anlık enaz akım	**:**	**0.000**	**m3/sn**	**14.11.1965**

Akımlar 01 Ekim 2005 'den 30 Eylül 2006' a kadar m3/sn olarak

Gün	Ekim	Kasım	Aralık	Ocak	Şubat	Mart	Nisan	Mayıs	Haziran	Temmuz	Ağustos	Eylül
01	0.245	0.760	0.544	0.544	0.544	0.596	4.07	5.66	1.00	0.400	0.280	0.360
02	0.245	0.760	0.544	0.544	0.544	0.596	4.07	8.00	1.00	0.400	0.280	0.360
03	0.245	0.596	0.544	0.544	0.544	0.596	4.18	8.64	0.880	0.400	0.280	0.360
04	0.245	0.400	0.544	0.544	0.544	0.700	4.53	8.48	0.880	0.400	0.280	0.360
05	0.280	0.400	0.544	0.544	0.544	0.700	5.38	8.16	0.544	0.648	0.280	0.360
06	0.280	0.400	0.544	0.544	0.544	0.648	5.94	8.00	0.210	0.648	0.280	0.360
07	0.280	0.400	0.544	0.544	0.544	0.648	6.65	8.16	0.210	0.648	0.280	0.360
08	0.280	0.400	0.544	0.544	0.544	0.648	6.50	8.64	0.210	0.544	0.280	0.360
09	0.280	0.400	0.544	0.544	0.544	0.700	6.50	8.32	0.210	0.360	0.280	0.360
10	0.280	0.245	0.544	0.544	0.544	0.820	6.65	7.85	0.210	0.320	0.280	0.360
11	0.280	0.155	0.544	0.544	0.544	1.24	6.50	6.95	0.280	0.320	0.280	0.360
12	0.280	0.183	0.544	0.544	0.544	1.58	6.36	6.08	0.280	0.320	0.280	0.360
13	0.280	0.400	0.544	0.544	0.544	1.76	6.08	5.80	0.280	0.280	0.245	0.360
14	0.280	0.544	0.544	0.544	0.544	1.85	5.66	5.52	0.280	0.245	0.245	0.320
15	0.360	0.544	0.544	0.544	0.544	1.85	5.24	5.24	0.280	0.245	0.245	0.360
16	0.440	0.544	0.544	0.544	0.544	1.85	5.10	5.10	0.360	0.245	0.245	0.440
17	0.320	0.544	0.544	0.544	0.544	1.95	4.53	4.99	0.400	0.245	0.280	0.492
18	0.320	0.544	0.544	0.544	0.544	2.25	4.41	4.87	0.360	0.245	0.492	0.492
19	0.320	0.544	0.544	0.544	0.544	2.15	4.41	4.76	0.360	0.245	0.544	0.492
20	0.320	0.544	0.544	0.544	0.544	2.35	4.41	4.53	0.360	0.245	0.492	0.492
21	0.320	0.544	0.544	0.544	0.544	2.35	4.41	3.51	0.360	0.245	0.440	0.544
22	0.320	0.544	0.544	0.544	0.544	2.25	4.53	3.18	0.400	0.280	0.440	0.492
23	0.320	0.544	0.544	0.544	0.544	2.15	4.64	3.07	0.400	0.544	0.360	0.400
24	0.320	0.544	0.544	0.544	0.544	2.35	4.64	2.96	0.400	0.544	0.280	0.360
25	0.320	0.544	0.544	0.544	0.544	2.45	4.41	2.85	0.400	0.544	0.320	0.360
26	0.320	0.544	0.544	0.544	0.544	2.45	4.30	2.65	0.400	0.400	0.320	0.492
27	0.320	0.544	0.544	0.544	0.544	2.55	4.53	2.15	0.400	0.280	0.320	0.684
28	0.320	0.544	0.544	0.544	0.544	2.65	4.76	1.24	0.400	0.280	0.320	0.684
29	0.320	0.544	0.544	0.544	-----	2.75	4.99	1.16	0.400	0.280	0.320	0.684
30	0.320	0.544	0.544	0.544	-----	2.96	4.99	1.16	0.400	0.280	0.360	0.632
31	0.440	-----	0.544	0.544	-----	3.51	-----	1.08	-----	0.280	0.360	-----
Maks.	0.440	0.760	0.544	0.544	0.544	3.62	6.80	8.96	1.00	0.648	0.544	0.684
Min.	0.245	0.155	0.544	0.544	0.544	0.596	4.07	1.08	0.210	0.210	0.245	0.320
Ortalama	0.306	0.492	0.544	0.544	0.544	1.74	5.11	5.12	0.418	0.366	0.322	0.437
LT/SN/Km2	1.64	2.63	2.91	2.91	2.91	9.31	27.4	27.4	2.24	1.96	1.72	2.34
AKIM mm.	4.39	6.82	7.80	7.80	7.04	24.9	70.9	73.4	5.81	5.25	4.62	6.06
MİL. M3	0.821	1.27	1.46	1.46	1.32	4.66	13.3	13.7	1.08	0.982	0.863	1.13

SU YILI (2006) YILLIK TOPLAM AKIM 42.05 MİLYON M3 225 MM. 7.1 LT/SN/Km2

23. Çoruh Havzasi

D23A016 ÇORUH N. MESCİTLİ

YERİ : ERZURUM İLİ PAZAR YOLU ILÇESİ 95 KM SİNDEN SOLA AYRILAN YOLUN 27 KM SİNDEKİ MESCİTLİ KÖYÜNDEDİR.
40°39'32" Doğu - 40°13'58" Kuzey

YAĞIŞ ALANI : 481,00 km2 **YAKLAŞIK KOT** : 1805 m

GÖZLEM SÜRESİ : 16.09.1965 - 30.09.2006

ORTALAMA AKIMLAR : Gözlem süresinde 5.891 m3/sn. (39 Yıllık) 2006 Su yılında 7.139 m3/sn.

ANLIK EN ÇOK VE EN AZ AKIMLAR:

2006 Su yılında anlık ençok akım	:	41.1	m3/sn	08.05.2006
2006 Su yılında anlık enaz akım	:	0.680	m3/sn	07.02.2006
Gözlem süresinde anlık ençok akım	:	68.0	m3/sn	10.04.1980
Gözlem süresinde anlık enaz akım	:	0.064	m3/sn	09.01.2003

23. Anahtar Eğrisi (Seviyeler cm olarak)

Seviye	Akım	Seviye	Akım	Seviye	Akım	Seviye	Akım
12	1.1	30	4.3	60	13.6	110	39.2
14	1.4	40	6.9	70	17.7	120	45.5
16	1.7	45	8.4	80	22.0	121	46.1
18	2.0	50	9.8	90	27.2	122	46.9
20	2.3	55	11.6	100	32.9	123	47.6

Akımlar 01 Ekim 2005 'den 30 Eylül 2006' a kadar m3/sn olarak

Gün	Ekim	Kasım	Aralık	Ocak	Şubat	Mart	Nisan	Mayıs	Haziran	Temmuz	Ağustos	Eylül
01	3.35	6.44	3.16	2.78	0.940	2.03	11.5	23.8	15.3	7.80	4.13	3.87
02	3.35	5.23	3.16	2.78	0.940	2.03	14.0	31.0	15.3	7.80	4.13	3.87
03	3.16	4.65	3.16	2.78	0.940	2.03	14.4	31.0	14.9	7.46	4.13	3.87
04	3.35	4.39	3.16	2.78	0.940	2.40	12.3	29.3	13.6	7.80	4.13	3.87
05	3.35	4.39	3.16	2.78	0.940	2.03	11.1	28.2	13.2	7.46	4.13	3.87
06	3.16	4.39	3.16	2.03	0.940	2.03	10.7	30.4	12.8	7.12	4.13	3.87
07	3.16	4.13	2.97	1.20	0.680	2.40	11.5	29.3	13.6	6.44	4.13	3.16
08	3.16	4.13	2.97	1.07	0.680	2.59	12.8	32.7	12.3	6.78	4.13	2.59
09	3.16	4.13	2.97	1.07	1.52	3.35	19.1	36.3	11.5	6.44	3.87	2.59
10	3.16	3.61	2.97	1.20	2.03	3.16	20.1	32.7	11.1	5.81	3.87	2.59
11	3.16	3.61	2.97	1.20	2.03	2.78	22.8	30.4	10.4	5.23	3.87	2.40
12	3.16	3.61	2.97	1.07	2.03	2.59	21.7	28.2	9.98	5.23	3.87	2.40
13	2.97	3.35	2.78	1.07	2.03	2.59	23.3	27.1	9.60	4.94	3.87	2.40
14	2.78	3.16	2.78	1.07	2.03	2.59	23.8	28.8	8.88	4.65	3.87	2.59
15	2.97	3.16	2.78	1.07	2.40	2.97	26.6	25.5	8.52	4.94	3.87	2.59
16	3.16	3.35	2.97	1.07	2.03	2.97	31.5	23.8	8.16	5.52	3.87	2.59
17	2.97	3.16	2.78	1.07	2.03	2.97	29.9	23.8	7.80	4.94	3.87	2.40
18	3.87	3.16	2.78	1.07	2.03	3.16	27.1	24.4	7.80	4.65	3.87	2.40
19	3.61	3.16	2.78	1.07	2.03	3.16	25.5	23.3	7.46	4.94	3.87	2.40
20	4.94	3.16	2.78	1.07	2.40	2.97	24.9	21.7	7.46	4.65	4.39	2.40
21	4.94	3.35	2.78	1.07	2.59	2.97	25.5	20.6	7.12	4.39	4.13	2.40
22	4.13	3.35	2.78	1.07	2.78	3.16	26.0	20.1	7.12	4.39	4.13	2.59
23	3.87	3.16	2.78	1.07	2.78	3.16	25.5	20.1	7.12	4.39	4.13	2.59
24	3.61	2.97	2.78	1.07	2.97	3.16	31.5	19.1	7.12	4.13	4.13	2.97
25	3.35	2.97	2.97	1.07	2.78	4.39	32.7	18.6	6.78	4.13	4.13	2.78
26	3.35	3.16	2.78	1.07	2.40	5.23	28.8	19.1	6.78	4.13	4.13	2.78
27	3.35	3.16	2.78	0.940	2.40	5.81	24.9	19.1	7.46	4.13	3.87	2.78
28	3.61	3.16	2.78	0.940	2.03	6.44	22.2	19.1	7.46	4.13	3.87	2.59
29	4.65	3.16	2.78	0.940	-----	6.78	20.6	17.7	8.16	4.13	3.87	2.59
30	4.39	3.35	2.78	0.940	-----	7.12	23.3	16.2	7.46	4.13	3.87	2.78
31	5.52	-----	2.78	0.940	-----	8.16	-----	15.3	-----	4.13	3.87	-----
Maks.	7.12	7.12	3.35	2.78	3.87	11.1	37.5	41.1	16.7	9.60	8.88	3.87
Min.	2.78	2.59	2.03	0.940	0.680	1.35	9.98	14.0	6.44	4.13	3.87	2.03
Ortalama	3.57	3.67	2.90	1.37	1.87	3.52	21.9	24.7	9.74	5.38	4.00	2.85
LT/SN/Km2	7.43	7.63	6.03	2.84	3.88	7.32	45.4	51.4	20.3	11.2	8.32	5.93
AKIM mm.	19.9	19.8	16.2	7.62	9.40	19.6	118.	138.	52.5	30.0	22.3	15.4
MİL. M3	9.57	9.52	7.77	3.67	4.52	9.43	56.6	66.2	25.2	14.4	10.7	7.39

SU YILI (2006) YILLIK TOPLAM AKIM 224.97 MİLYON M3 468 MM. 14.8 LT/SN/Km2

23. Çoruh Havzasi

D23A026 BÜYÜKÇAY UZUN KAVAK

YERİ : ERZURUM ARTVİN KARAYOLUNUN 70 KM SİNDEN SOLA AYRILAN YOLUN 27 KM SİNDEKİ SERDARLI NAHİYESİNDEDİR.
41°15'0" Doğu - 40°29'0" Kuzey

YAĞIŞ ALANI : 110,00 km2 **YAKLAŞIK KOT** : 1850 m

GÖZLEM SÜRESİ : 01.10.1979 - 30.09.2006

ORTALAMA AKIMLAR : Gözlem süresinde 1.943 m3/sn. (26 Yıllık) 2006 Su yılında 1.953 m3/sn.

ANLIK EN ÇOK VE EN AZ AKIMLAR:

2006 Su yılında anlık ençok akım	:	13.2	m3/sn	17.05.2006
2006 Su yılında anlık enaz akım	:	0.360	m3/sn	21.02.2006
Gözlem süresinde anlık ençok akım	:	28.8	m3/sn	24.05.1996
Gözlem süresinde anlık enaz akım	:	0.003	m3/sn	01.09.1992

12. Anahtar Eğrisi (Seviyeler cm olarak)

Seviye	Akım	Seviye	Akım	Seviye	Akım	Seviye	Akım
10	0.197	54	4.4	99	14.8	145	33.6
18	0.567	63	5.9	108	17.8	153	38.2
27	1.2	72	7.7	117	21.1	163	44.1
36	2.0	81	9.7	127	25.0	172	49.9
45	3.1	90	12.2	136	29.2	182	56.9

Akımlar 01 Ekim 2005 'den 30 Eylül 2006' a kadar m3/sn olarak

Gün	Ekim	Kasım	Aralık	Ocak	Şubat	Mart	Nisan	Mayıs	Haziran	Temmuz	Ağustos	Eylül
01	0.944	1.13	0.850	1.80	0.640	0.640	0.640	4.79	6.51	2.89	1.23	0.850
02	0.944	1.04	0.850	1.80	0.640	0.640	0.640	4.95	6.32	2.89	1.23	0.850
03	0.944	1.04	0.944	1.80	0.640	0.640	0.640	4.95	5.93	2.61	1.23	0.850
04	0.944	1.04	0.944	1.80	0.640	0.640	0.640	5.15	5.93	2.61	1.13	0.850
05	0.944	1.04	0.944	1.80	0.640	0.640	0.640	5.34	5.54	2.61	1.13	0.850
06	0.850	1.04	0.944	1.23	0.640	0.640	0.850	5.73	5.54	2.47	1.13	0.850
07	0.850	1.04	0.850	0.575	0.640	0.640	1.04	6.90	5.73	2.47	1.04	0.850
08	0.850	1.04	0.850	0.710	0.640	0.640	1.32	8.20	5.54	2.47	1.04	0.850
09	0.850	0.944	0.850	0.710	0.640	0.710	1.32	7.68	5.15	2.33	1.04	0.780
10	0.850	0.850	0.850	0.710	0.640	0.640	2.75	7.94	4.79	2.20	1.04	0.780
11	0.850	0.850	0.850	0.710	0.640	0.640	2.75	7.42	4.46	2.06	1.04	0.780
12	0.850	0.850	0.780	0.710	0.640	0.640	3.16	7.94	4.13	1.92	0.944	0.850
13	0.780	0.850	0.780	0.640	0.640	0.640	4.13	8.98	3.80	1.80	0.944	0.850
14	0.850	0.850	0.780	0.640	0.640	0.640	4.29	9.50	3.63	1.80	0.944	0.850
15	0.850	0.850	0.780	0.640	0.640	0.640	4.29	8.72	3.63	1.80	0.944	0.850
16	0.850	0.850	0.780	0.710	0.640	0.640	4.95	8.72	3.30	1.68	0.944	0.780
17	1.13	0.850	0.780	0.850	0.780	0.640	5.34	9.77	3.16	1.56	0.944	0.780
18	0.944	0.780	0.780	0.850	0.944	0.640	5.93	8.72	3.16	1.44	0.944	0.780
19	1.13	0.850	0.780	0.850	0.944	0.640	5.54	7.94	3.16	1.56	0.944	0.780
20	1.13	0.850	0.780	0.850	0.710	0.640	4.95	7.42	3.02	1.44	0.944	0.780
21	1.04	0.780	0.780	0.850	0.510	0.640	4.29	8.20	3.02	1.44	1.13	0.780
22	1.04	0.850	0.780	0.850	0.640	0.640	3.96	8.46	2.75	1.44	1.04	0.780
23	0.944	0.850	0.780	0.850	0.640	0.640	3.80	8.46	2.75	1.32	1.04	0.850
24	0.944	0.850	0.780	0.850	0.640	0.640	3.80	8.46	2.61	1.32	0.944	0.850
25	0.944	0.780	0.780	0.850	0.640	0.640	3.63	8.72	2.61	1.32	0.944	0.850
26	0.944	0.780	0.780	0.640	0.640	0.640	3.63	8.46	2.75	1.32	0.944	0.850
27	0.944	0.780	1.44	0.510	0.640	0.640	3.47	8.20	2.89	1.32	0.944	0.850
28	1.04	0.850	1.80	0.575	0.640	0.640	3.30	7.68	3.02	1.32	0.850	0.850
29	1.04	0.780	1.80	0.640	-----	0.640	3.47	6.32	2.89	1.32	0.850	0.780
30	0.944	0.850	1.80	0.640	-----	0.640	4.29	6.51	2.75	1.23	0.850	0.944
31	1.13	-----	1.80	0.640	-----	0.640	-----	6.51	-----	1.23	0.850	-----
Maks.	1.32	1.23	1.80	1.80	0.944	0.710	5.93	13.2	6.90	4.62	1.68	1.13
Min.	0.780	0.710	0.710	0.410	0.360	0.640	0.640	3.63	2.33	1.13	0.850	0.710
Ortalama	0.945	0.893	0.970	0.912	0.665	0.642	3.12	7.51	4.02	1.84	1.01	0.827
LT/SN/Km2	8.59	8.12	8.82	8.29	6.04	5.84	28.3	68.3	36.5	16.8	9.14	7.52
AKIM mm.	23.0	21.0	23.6	22.2	14.6	15.6	73.4	183.	94.6	44.9	24.5	19.5
MİL. M3	2.53	2.31	2.60	2.44	1.61	1.72	8.07	20.1	10.4	4.94	2.69	2.14

SU YILI (2006) YILLIK TOPLAM AKIM 61.55 MİLYON M3 560 MM. 17.8 LT/SN/Km2

23. Çoruh Havzasi

D23A028 BÜYÜKÇAY ÇATIKSU

YERİ : **BAYBURT TRABZON YOLUNUN 30. KM SİNDEKİ OSLUK KÖPRÜSÜNÜN 10 KM MENBAĞINDADIR. 40°3'47" Doğu - 40°24'11" Kuzey**

YAĞIŞ ALANI : **1440,00 km2** **YAKLAŞIK KOT : 1600 m**

GÖZLEM SÜRESİ : **01.10.1980 - 30.09.2006**

ORTALAMA AKIMLAR : **Gözlem süresinde 6.093 m3/sn. (23 Yıllık) 2006 Su yılında 9.987 m3/sn.**

ANLIK EN ÇOK VE EN AZ AKIMLAR:

2006 Su yılında anlık ençok akım	**:**	**67.5**	**m3/sn**	**09.05.2006**
2006 Su yılında anlık enaz akım	**:**	**1.51**	**m3/sn**	**15.08.2006**
Gözlem süresinde anlık ençok akım	**:**	**82.0**	**m3/sn**	**15.04.2005**
Gözlem süresinde anlık enaz akım	**:**	**0.100**	**m3/sn**	**13.01.1981**

Akımlar 01 Ekim 2005 'den 30 Eylül 2006' a kadar m3/sn olarak

Gün	Ekim	Kasım	Aralık	Ocak	Şubat	Mart	Nisan	Mayıs	Haziran	Temmuz	Ağustos	Eylül
01	1.99	18.2	4.23	3.21	2.17	2.72	28.9	47.9	13.0	4.85	2.17	1.76
02	1.99	12.3	4.03	3.21	2.17	3.00	33.6	55.7	12.0	5.58	2.17	1.76
03	1.99	9.52	4.03	3.21	2.03	3.62	37.4	62.7	11.0	5.58	2.17	1.76
04	1.99	9.00	4.03	3.21	1.90	4.23	38.8	62.1	9.52	5.58	2.17	1.76
05	1.99	8.48	4.03	3.21	2.31	4.23	35.5	56.8	8.48	5.32	2.17	1.76
06	1.99	8.22	4.03	3.21	2.31	4.44	33.6	56.3	7.70	5.85	2.17	1.90
07	1.99	7.70	3.62	3.21	2.31	4.85	32.2	55.2	7.17	6.11	2.17	1.90
08	1.99	4.44	3.62	2.86	2.31	6.91	32.2	56.8	6.91	6.38	2.17	1.90
09	1.99	5.32	3.62	2.72	2.45	14.8	38.8	65.9	6.11	6.64	2.17	1.90
10	1.99	7.17	3.62	2.59	2.45	15.6	42.6	59.5	5.32	6.11	2.17	1.90
11	1.99	6.91	3.62	2.59	2.31	12.3	45.5	54.1	4.85	5.58	2.17	1.90
12	1.99	6.64	3.62	2.59	2.31	11.3	46.9	49.3	4.85	5.05	1.90	1.90
13	1.99	6.38	3.62	2.59	2.31	10.3	45.0	45.5	4.64	4.64	1.90	1.90
14	1.99	6.11	3.41	2.45	2.31	10.0	43.6	44.1	4.44	4.23	1.90	1.90
15	1.99	5.85	3.41	2.45	2.31	12.0	42.2	40.7	4.03	4.03	1.51	2.03
16	1.99	5.85	3.41	2.31	2.31	12.0	42.2	36.9	4.03	3.62	1.62	2.17
17	1.99	5.58	3.41	2.31	2.31	12.0	41.7	34.5	3.62	3.41	1.51	1.90
18	1.99	5.58	3.41	2.31	2.31	12.7	39.3	32.2	3.62	3.00	1.62	1.90
19	2.25	5.58	3.41	2.31	2.45	13.7	35.5	32.7	3.41	2.86	1.51	1.90
20	3.34	5.05	3.41	2.31	2.31	13.4	32.7	29.4	3.41	2.72	1.62	1.90
21	3.34	5.05	3.41	2.31	2.31	12.3	33.6	27.0	3.62	2.59	1.90	1.90
22	2.93	4.85	3.41	2.31	2.31	12.0	34.5	24.8	3.41	2.59	2.03	1.90
23	2.93	4.64	3.41	2.31	2.31	12.3	35.0	23.1	3.21	2.45	2.03	2.03
24	2.76	4.44	3.21	2.31	2.31	12.7	38.8	21.5	3.21	2.17	2.03	2.03
25	2.76	4.23	3.21	2.31	2.31	15.9	39.3	20.3	3.62	2.17	2.03	2.03
26	2.76	4.23	3.21	2.31	2.45	22.7	38.8	19.0	4.03	2.17	2.03	2.03
27	2.59	4.23	3.21	2.17	2.45	22.3	35.5	17.4	4.23	2.17	2.03	2.03
28	2.59	4.23	3.21	2.17	2.45	21.5	32.2	18.6	4.44	2.17	1.90	2.03
29	2.76	4.23	3.21	2.17	-----	21.9	30.3	18.6	4.64	2.17	1.90	2.03
30	3.10	4.23	3.21	2.17	-----	21.9	43.6	16.3	4.64	2.17	1.90	2.03
31	7.09	-----	3.21	2.17	-----	23.6	-----	14.8	-----	2.17	1.90	-----
Maks.	18.2	20.3	4.23	3.21	3.00	25.6	50.9	67.5	13.7	6.64	2.17	2.31
Min.	1.99	4.23	3.21	2.17	1.76	2.59	25.6	13.7	3.00	2.17	1.51	1.76
Ortalama	2.48	6.47	3.53	2.57	2.31	12.4	37.7	38.7	5.57	3.94	1.96	1.92
LT/SN/Km2	1.73	4.50	2.45	1.78	1.60	8.58	26.2	26.9	3.87	2.74	1.36	1.34
AKIM mm.	4.62	11.7	6.57	4.77	3.87	23.0	67.8	72.0	10.0	7.33	3.64	3.46
MİL. M3	6.65	16.8	9.46	6.87	5.58	33.1	97.6	104.	14.4	10.6	5.24	4.99

SU YILI (2006) YILLIK TOPLAM AKIM 315.29 MİLYON M3 219 MM. 6.9 LT/SN/Km2

23. Çoruh Havzasi

D23A029 HAHO D. GÖLDERE

YERİ : **BAYBURT-ERZİNCAN YOLUNUN 8. KM SİNDEN SOLA AYRILAN YOLU TAKİBEN 14. KM DE GÖLDERE MEVKİİNDE.**
40°6'30" Doğu - 40°7'10" Kuzey

YAĞIŞ ALANI : **88,52 km2** **YAKLAŞIK KOT : 1760 m**

GÖZLEM SÜRESİ : **01.10.1982 - 30.09.2006**

ORTALAMA AKIMLAR : **Gözlem süresinde 0.667 m3/sn. (24 Yıllık) 2006 Su yılında 0.914 m3/sn.**

ANLIK EN ÇOK VE EN AZ AKIMLAR:

2006 Su yılında anlık ençok akım	**:**	**4.30 m3/sn**	**08.05.2006**
2006 Su yılında anlık enaz akım	**:**	**0.258 m3/sn**	**01.10.2005**
Gözlem süresinde anlık ençok akım	**:**	**6.83 m3/sn**	**27.04.1997**
Gözlem süresinde anlık enaz akım	**:**	**0.021 m3/sn**	**10.10.1993**

Akımlar 01 Ekim 2005 'den 30 Eylül 2006' a kadar m3/sn olarak

Gün	Ekim	Kasım	Aralık	Ocak	Şubat	Mart	Nisan	Mayıs	Haziran	Temmuz	Ağustos	Eylül
01	0.258	1.50	0.350	0.490	1.35	0.350	1.30	3.50	1.05	0.660	0.350	0.300
02	0.258	1.05	0.350	0.660	0.732	0.350	1.55	3.50	1.05	0.660	0.350	0.300
03	0.258	0.840	0.350	0.660	1.05	0.350	1.85	3.50	1.05	0.660	0.350	0.300
04	0.258	0.804	0.350	0.660	1.10	0.350	1.85	3.50	0.840	0.660	0.350	0.300
05	0.258	0.732	0.350	0.625	0.660	0.350	1.85	3.50	0.840	0.660	0.350	0.300
06	0.258	0.732	0.350	0.430	0.490	0.350	1.85	3.50	0.840	0.660	0.350	0.300
07	0.258	0.732	0.350	0.350	0.350	0.375	1.85	3.50	0.840	0.660	0.350	0.300
08	0.258	0.660	0.350	0.350	0.350	0.660	1.85	3.90	0.660	0.660	0.350	0.300
09	0.258	0.660	0.350	0.325	0.490	0.924	1.91	4.30	0.660	0.660	0.350	0.300
10	0.258	0.660	0.350	0.350	0.660	0.840	2.61	4.30	0.660	0.590	0.350	0.300
11	0.258	0.660	0.350	0.350	0.660	0.660	3.42	4.22	0.660	0.490	0.350	0.300
12	0.258	0.660	0.350	0.350	0.660	0.660	3.50	3.58	0.660	0.430	0.350	0.300
13	0.258	0.660	0.350	0.350	0.696	0.660	3.50	3.50	0.660	0.350	0.350	0.300
14	0.258	0.490	0.350	0.350	1.01	0.660	3.50	3.50	0.660	0.350	0.350	0.300
15	0.258	0.490	0.350	0.350	0.840	0.660	3.50	3.42	0.660	0.350	0.350	0.300
16	0.258	0.490	0.350	0.350	0.660	0.660	3.50	2.80	0.490	0.350	0.350	0.300
17	0.325	0.490	0.350	0.555	0.660	0.660	3.42	2.72	0.490	0.350	0.350	0.300
18	0.350	0.350	0.350	1.10	0.660	0.660	2.80	2.72	0.490	0.350	0.350	0.300
19	0.350	0.350	0.350	1.73	0.840	0.660	2.72	2.72	0.490	0.350	0.350	0.300
20	0.350	0.350	0.350	1.85	0.840	0.660	2.72	2.44	0.490	0.350	0.350	0.300
21	0.350	0.350	0.350	2.03	0.732	0.660	2.72	2.32	0.490	0.350	0.350	0.300
22	0.350	0.350	0.350	2.32	0.375	0.660	2.72	2.15	0.490	0.350	0.350	0.300
23	0.350	0.350	0.350	2.80	0.350	0.660	2.80	2.15	0.490	0.350	0.350	0.300
24	0.325	0.350	0.350	2.32	0.350	0.840	3.42	1.85	0.490	0.350	0.350	0.300
25	0.300	0.350	0.350	2.03	0.350	0.840	3.50	1.85	0.490	0.350	0.350	0.300
26	0.300	0.350	0.350	2.66	0.350	1.05	3.11	1.55	0.490	0.350	0.350	0.300
27	0.300	0.350	0.350	2.61	0.350	1.05	2.72	1.55	0.490	0.350	0.300	0.300
28	0.300	0.350	0.350	1.67	0.350	1.05	2.72	1.55	0.490	0.350	0.300	0.300
29	0.350	0.350	0.490	1.55	-----	1.05	2.72	1.30	0.660	0.350	0.300	0.300
30	0.460	0.350	0.490	1.67	-----	1.05	2.61	1.30	0.696	0.350	0.300	0.300
31	0.590	-----	0.490	1.79	-----	1.05	-----	1.45	-----	0.375	0.300	-----
Maks.	1.05	1.55	0.490	3.11	1.79	1.05	3.50	4.30	1.05	0.660	0.350	0.300
Min.	0.258	0.350	0.350	0.300	0.350	0.350	1.30	1.30	0.490	0.350	0.300	0.300
Ortalama	0.306	0.562	0.364	1.15	0.642	0.692	2.67	2.83	0.651	0.456	0.342	0.300
LT/SN/Km2	3.45	6.35	4.11	13.0	7.25	7.82	30.2	31.9	7.35	5.15	3.86	3.39
AKIM mm.	9.25	16.5	11.0	34.8	17.5	20.9	78.2	85.5	19.0	13.8	10.3	8.78
MİL. M3	0.819	1.46	0.974	3.08	1.55	1.85	6.92	7.57	1.69	1.22	0.916	0.778

SU YILI (2006) YILLIK TOPLAM AKIM 28.83 MİLYON M3 326 MM. 10.3 LT/SN/Km2

23. Çoruh Havzasi

D23A031 KONAK D. SIRAKONAK

YERİ : **ERZURUM ARTVİN KARAYOLUNUN 55 KM SİNDEN SOLA AYRILAN YOLUN 17 KM SİNDEDİR.**
41°22'51" Doğu - 40°17'41" Kuzey

YAĞIŞ ALANI : **60,01 km2** **YAKLAŞIK KOT : 1740 m**

GÖZLEM SÜRESİ : **01.10.1985 - 30.09.2006**

ORTALAMA AKIMLAR : **Gözlem süresinde 1.278 m3/sn. (21 Yıllık) 2006 Su yılında 1.288 m3/sn.**

ANLIK EN ÇOK VE EN AZ AKIMLAR:

2006 Su yılında anlık ençok akım	:	**8.65**	**m3/sn**	**08.05.2006**
2006 Su yılında anlık enaz akım	:	**0.037**	**m3/sn**	**02.02.2006**
Gözlem süresinde anlık ençok akım	:	**19.2**	**m3/sn**	**24.04.2005**
Gözlem süresinde anlık enaz akım	:	**0.037**	**m3/sn**	**02.02.2006**

İstasyon için kullanılmış anahtar bulunamadı.

Akımlar 01 Ekim 2005 'den 30 Eylül 2006' a kadar m3/sn olarak

Gün	Ekim	Kasım	Aralık	Ocak	Şubat	Mart	Nisan	Mayıs	Haziran	Temmuz	Ağustos	Eylül
01	0.492	1.15	0.708	0.371	0.420	0.564	1.63	2.45	4.21	0.904	0.430	0.258
02	0.420	1.02	0.708	0.636	0.371	0.564	1.63	3.43	4.40	0.983	0.430	0.215
03	0.420	0.902	0.780	0.564	0.492	0.636	1.63	3.43	4.40	0.983	0.430	0.215
04	0.492	0.902	0.780	0.564	0.492	0.564	1.39	3.43	4.21	1.06	0.387	0.215
05	0.492	0.902	0.780	0.564	0.492	0.564	1.27	3.62	3.82	0.983	0.344	0.215
06	0.420	0.902	0.780	0.564	0.492	0.564	1.27	3.62	3.62	0.904	0.430	0.301
07	0.492	0.902	0.780	0.564	0.492	0.636	1.27	4.67	3.82	0.904	0.301	0.301
08	0.492	0.902	0.708	0.564	0.492	0.636	1.51	6.29	3.23	0.983	0.344	0.301
09	0.492	0.780	0.708	0.564	0.492	0.708	2.76	6.56	2.84	0.904	0.344	0.301
10	0.492	0.780	0.708	0.564	0.492	0.636	3.14	5.75	2.45	0.825	0.301	0.344
11	0.492	0.780	0.708	0.564	0.492	0.636	3.52	5.75	2.33	0.746	0.258	0.301
12	0.492	0.708	0.708	0.564	0.492	0.636	3.71	5.48	2.20	0.746	0.258	0.344
13	0.564	0.708	0.636	0.564	0.492	0.636	3.90	6.02	1.96	0.746	0.258	0.344
14	0.564	0.708	0.636	0.564	0.492	0.636	4.15	6.29	1.71	0.746	0.301	0.344
15	0.564	0.708	0.636	0.564	0.492	0.708	4.90	5.75	1.59	0.667	0.344	0.344
16	0.564	0.708	0.708	0.708	0.492	0.708	4.40	5.21	1.47	0.667	0.344	0.430
17	1.02	0.708	0.636	0.636	0.708	0.708	4.01	6.02	1.34	0.667	0.301	0.588
18	0.708	0.708	0.708	0.322	0.780	0.708	3.62	5.75	1.14	0.667	0.301	0.509
19	1.02	0.708	0.708	0.322	0.492	0.708	3.43	5.21	0.825	0.667	0.387	0.509
20	1.02	0.708	0.708	0.371	0.492	0.636	3.23	4.67	1.06	0.667	0.387	0.430
21	0.780	0.708	0.708	0.420	0.492	0.564	3.43	4.67	1.34	0.667	0.509	0.430
22	0.708	0.708	0.636	0.420	0.492	0.564	3.62	4.94	1.22	0.746	0.509	0.509
23	0.708	0.636	0.708	0.492	0.492	0.636	3.82	4.94	1.22	0.667	0.509	0.588
24	0.708	0.636	0.708	0.492	0.492	0.708	4.21	4.67	1.06	0.667	0.344	0.588
25	0.708	0.708	0.708	0.492	0.492	1.02	4.67	4.94	0.983	0.667	0.301	0.588
26	0.708	0.708	0.636	0.492	0.492	1.02	3.62	4.94	0.983	0.667	0.258	0.588
27	0.708	0.708	0.780	0.492	0.564	1.02	3.04	5.21	1.06	0.667	0.258	0.588
28	0.780	0.708	0.636	0.492	0.564	1.02	2.33	5.21	1.06	0.667	0.215	0.588
29	0.902	0.708	0.564	0.564	-----	1.15	2.20	4.67	0.983	0.667	0.215	0.509
30	0.902	0.780	0.564	0.902	-----	1.15	2.33	4.40	0.983	0.588	0.258	0.588
31	0.780	-----	0.322	0.420	-----	1.39	-----	4.40	-----	0.509	0.258	-----
Maks.	1.51	1.27	1.27	1.88	1.51	1.76	5.48	8.65	6.56	1.59	1.22	0.667
Min.	0.420	0.492	0.072	0.148	0.037	0.564	1.27	2.33	0.746	0.387	0.215	0.187
Ortalama	0.649	0.777	0.684	0.528	0.508	0.743	2.99	4.92	2.12	0.761	0.339	0.412
LT/SN/Km2	10.8	12.9	11.4	8.80	8.47	12.4	49.8	81.9	35.3	12.7	5.65	6.87
AKIM mm.	28.9	33.5	30.5	23.6	20.5	33.2	129.	219.	91.4	34.0	15.1	17.8
MİL. M3	1.74	2.01	1.83	1.41	1.23	1.99	7.74	13.2	5.49	2.04	0.908	1.07

SU YILI (2006) YILLIK TOPLAM AKIM 40.66 MİLYON M3 678 MM. 21.5 LT/SN/Km2

23. Çoruh Havzasi

D23A032 TEPE D. YELLİ TEPE

YERİ : ERZURUM ARTVİN KARAYOLUNUN 55 KM SİNDEN SOLA AYRILAN YOLUN 17 KM SİNDEDİR.
41°22'48" Doğu - 40°17'35" Kuzey

YAĞIŞ ALANI : 153,48 km2 **YAKLAŞIK KOT** : 1740 m

GÖZLEM SÜRESİ : 01.10.1985 - 30.09.2006

ORTALAMA AKIMLAR : Gözlem süresinde 2.301 m3/sn. (21 Yıllık) 2006 Su yılında 2.199 m3/sn.

ANLIK EN ÇOK VE EN AZ AKIMLAR:

2006 Su yılında anlık ençok akım	:	17.0	m3/sn	08.05.2006
2006 Su yılında anlık enaz akım	:	0.576	m3/sn	05.08.2006
Gözlem süresinde anlık ençok akım	:	53.5	m3/sn	16.05.1991
Gözlem süresinde anlık enaz akım	:	0.218	m3/sn	11.07.2003

11. Anahtar Eğrisi (Seviyeler cm olarak)

Seviye	Akım	Seviye	Akım	Seviye	Akım	Seviye	Akım
70	0.001	97	2.3	117	6.3	137	11.7
81	0.515	101	3.0	121	7.2	150	15.9
85	0.868	105	3.7	125	8.3	160	19.1
89	1.3	109	4.5	129	9.3	170	22.3
93	1.8	113	5.3	133	10.5	180	25.5

Akımlar 01 Ekim 2005 'den 30 Eylül 2006' a kadar m3/sn olarak

Gün	Ekim	Kasım	Aralık	Ocak	Şubat	Mart	Nisan	Mayıs	Haziran	Temmuz	Ağustos	Eylül
01	1.01	1.75	1.33	0.800	0.905	1.12	2.51	4.22	4.22	1.85	1.43	0.996
02	0.905	1.64	1.33	1.22	0.800	1.12	2.68	6.85	4.60	2.35	1.64	1.10
03	0.905	1.54	1.43	1.12	1.01	1.22	2.68	7.72	4.60	2.35	1.10	0.996
04	0.905	1.54	1.43	1.12	1.01	1.12	2.35	7.41	4.22	2.18	0.996	1.10
05	0.905	1.54	1.43	1.12	1.01	1.12	2.18	7.41	3.84	2.18	0.780	1.21
06	0.905	1.54	1.43	1.12	1.01	1.12	2.02	8.65	4.22	1.85	0.678	1.21
07	1.01	1.54	1.43	1.12	1.01	1.22	2.02	9.89	4.41	1.75	0.678	1.21
08	1.01	1.43	1.33	1.12	1.01	1.22	2.35	11.4	4.45	1.75	0.576	1.10
09	1.01	1.43	1.33	1.12	1.01	1.33	3.50	11.0	4.26	1.64	0.678	1.10
10	1.01	1.43	1.33	1.12	1.01	1.22	3.88	10.2	3.88	1.64	0.678	0.996
11	1.01	1.43	1.33	1.12	1.01	1.22	4.26	9.27	3.69	1.54	0.780	1.10
12	1.01	1.33	1.33	1.12	1.01	1.22	4.45	8.96	3.50	1.33	1.10	1.21
13	1.12	1.33	1.22	1.12	1.01	1.22	4.83	9.27	3.17	1.33	0.996	1.21
14	1.12	1.33	1.22	1.12	1.01	1.22	5.40	8.65	3.01	1.22	0.996	1.21
15	1.12	1.33	1.22	1.12	1.01	1.33	7.48	7.72	2.68	1.22	0.888	1.21
16	1.12	1.33	1.33	1.33	1.01	1.33	10.2	7.41	2.51	1.33	0.996	1.21
17	1.64	1.33	1.22	1.22	1.22	1.33	8.34	7.72	2.35	1.22	0.996	1.21
18	1.33	1.33	1.33	0.800	1.43	1.33	7.10	7.10	2.18	1.12	1.21	1.21
19	1.64	1.33	1.33	0.800	1.01	1.33	6.35	6.10	2.02	1.12	1.32	1.21
20	1.64	1.33	1.33	0.905	1.01	1.33	6.60	5.85	2.18	1.12	1.21	1.10
21	1.43	1.33	1.33	1.01	1.01	1.22	8.03	5.85	2.18	1.12	1.32	1.21
22	1.33	1.33	1.22	1.01	1.01	1.33	8.34	5.85	1.85	1.12	1.32	1.21
23	1.33	1.22	1.33	1.01	1.01	1.33	8.34	5.60	1.85	1.01	1.46	1.32
24	1.33	1.22	1.33	1.01	1.01	1.54	9.89	5.60	1.85	1.01	1.21	1.32
25	1.33	1.33	1.33	1.01	1.01	1.85	7.72	5.35	1.75	1.01	1.21	1.10
26	1.33	1.33	1.22	1.01	1.01	1.85	5.60	5.35	1.85	1.01	1.21	1.10
27	1.33	1.33	1.43	1.12	1.12	1.85	4.41	5.35	1.85	1.12	1.21	0.996
28	1.43	1.33	1.22	1.12	1.12	1.75	3.65	5.60	2.18	1.43	1.21	0.888
29	1.54	1.33	1.33	1.12	-----	1.75	3.27	4.85	2.18	1.43	1.21	0.780
30	1.54	1.22	1.33	1.33	-----	1.85	3.84	4.41	1.85	1.43	1.21	0.888
31	1.54	-----	1.12	1.22	-----	2.02	-----	4.22	-----	1.43	1.10	-----
Maks.	1.64	1.75	1.43	1.33	1.43	2.35	11.8	17.0	7.72	3.69	1.73	1.60
Min.	0.800	1.22	1.12	0.800	0.800	1.12	2.02	3.65	1.75	1.01	0.576	0.780
Ortalama	1.22	1.39	1.32	1.08	1.03	1.39	5.14	7.12	2.98	1.46	1.08	1.12
LT/SN/Km2	7.94	9.07	8.59	7.06	6.71	9.04	33.5	46.4	19.4	9.50	7.02	7.32
AKIM mm.	21.3	23.5	23.0	18.9	16.2	24.2	86.8	124.	50.3	25.5	18.8	19.0
MİL. M3	3.26	3.61	3.53	2.90	2.49	3.72	13.3	19.1	7.72	3.91	2.89	2.91

SU YILI (2006) YILLIK TOPLAM AKIM 69.34 MİLYON M3 452 MM. 14.3 LT/SN/Km2

23. Çoruh Havzasi

D23A037 BAŞKALE D. YANIKTAŞ

YERİ : NARMAN HASANKALE YOLUNUN 10 KM SİNDE YANIKTAŞ KÖYÜNDEDİR.
41°51'36" Doğu - 40°16'15" Kuzey

YAĞIŞ ALANI : 207,60 km2 **YAKLAŞIK KOT** : 1625 m

GÖZLEM SÜRESİ : 01.10.1990 - 30.09.2006

ORTALAMA AKIMLAR : Gözlem süresinde 1.450 m3/sn. (15 Yıllık) 2006 Su yılında ---- m3/sn.

ANLIK EN ÇOK VE EN AZ AKIMLAR:

2006 Su yılında anlık ençok akım : ----- m3/sn

2006 Su yılında anlık enaz akım : ----- m3/sn

Gözlem süresinde anlık ençok akım : 35.2 m3/sn 06.03.2004

Gözlem süresinde anlık enaz akım : 0.005 m3/sn 23.02.2002

11. Anahtar Eğrisi (Seviyeler cm olarak)

Seviye	Akım	Seviye	Akım	Seviye	Akım	Seviye	Akım
22	0.039	32	0.271	50	1.7	110	19.5
24	0.067	34	0.356	60	3.3	120	23.9
26	0.103	36	0.455	70	5.6	130	28.4
28	0.147	38	0.572	80	8.5	140	32.9
30	0.203	40	0.709	100	15.4	150	38.0

Akımlar 01 Ekim 2005 'den 30 Eylül 2006' a kadar m3/sn olarak

Gün	Ekim	Kasım	Aralık	Ocak	Şubat	Mart	Nisan	Mayıs	Haziran	Temmuz	Ağustos	Eylül
01	0.411	3.19	0.810	0.810	0.810	0.740	-----	KURU	2.68	2.50	0.335	0.203
02	0.362	2.34	0.810	0.810	0.810	0.810	-----	KURU	2.85	1.89	0.415	0.203
03	0.362	1.88	0.929	0.810	0.810	0.810	-----	KURU	3.02	1.59	0.528	0.203
04	0.362	1.64	1.17	0.810	0.810	0.810	-----	KURU	2.51	1.59	0.370	0.180
05	0.411	1.64	1.05	0.810	0.810	0.740	-----	KURU	2.17	1.49	0.335	0.180
06	0.362	1.64	1.05	0.810	0.810	0.740	-----	10.8	2.17	1.28	0.300	0.203
07	0.362	1.64	0.929	0.810	0.810	0.810	-----	11.6	2.34	1.10	0.300	0.203
08	0.362	1.64	0.810	0.810	0.810	0.929	-----	12.3	2.17	0.952	0.263	0.225
09	0.362	1.52	0.810	0.810	0.530	1.29	-----	12.3	2.00	0.876	0.225	0.225
10	0.362	1.41	0.810	0.810	0.530	1.17	-----	12.3	2.00	0.800	0.225	0.225
11	0.362	1.29	0.810	0.810	0.530	0.929	-----	11.6	2.00	0.732	0.225	0.225
12	0.362	1.17	0.740	0.810	0.530	0.929	-----	10.8	2.00	0.664	0.225	0.225
13	0.362	1.17	0.740	0.810	0.530	0.929	-----	10.5	2.00	0.596	0.225	0.225
14	0.313	1.05	0.740	0.810	0.530	0.810	-----	10.1	1.64	0.528	0.180	0.225
15	0.362	0.929	0.740	0.810	0.530	0.810	-----	9.71	1.17	0.528	0.153	0.225
16	0.362	0.929	0.810	0.810	0.530	0.810	-----	9.34	1.17	0.732	0.153	0.225
17	2.00	0.929	0.740	0.810	0.530	KURU	-----	9.34	1.05	0.596	0.153	0.225
18	0.929	0.810	0.740	0.810	0.530	KURU	-----	9.34	1.05	0.596	0.180	0.225
19	0.810	0.810	0.740	0.810	0.530	KURU	-----	9.34	1.05	0.528	0.180	0.225
20	1.29	0.810	0.740	0.810	0.530	KURU	-----	9.34	0.929	0.528	0.225	0.225
21	0.929	0.929	0.740	0.810	0.530	KURU	-----	9.34	0.929	0.460	0.300	0.225
22	0.810	0.810	0.670	0.810	0.530	KURU	-----	9.34	0.810	0.528	0.300	0.225
23	0.740	0.740	0.740	0.810	0.530	KURU	-----	9.34	0.810	0.460	0.263	0.263
24	0.670	0.929	0.740	0.810	0.530	KURU	-----	9.34	0.810	0.460	0.263	0.263
25	0.600	0.740	0.810	0.810	0.530	KURU	-----	9.34	0.740	0.370	0.263	0.263
26	0.530	0.740	0.810	0.810	0.530	KURU	-----	4.70	0.740	0.370	0.263	0.263
27	0.530	0.810	0.810	0.810	0.670	KURU	-----	3.36	0.740	0.335	0.225	0.263
28	0.530	0.810	0.810	0.810	0.670	KURU	-----	3.19	1.05	0.335	0.225	0.225
29	0.810	0.810	0.810	0.810	-----	KURU	-----	3.19	1.17	0.415	0.225	0.225
30	1.05	0.929	0.810	0.810	-----	KURU	-----	2.85	2.51	0.415	0.225	0.263
31	2.68	-----	0.810	0.810	-----	KURU	-----	2.68	-----	0.370	0.203	-----
Maks.	4.30	3.70	1.17	0.810	0.810	1.41	--	13.6	14.0	5.10	0.952	0.335
Min.	0.313	0.600	0.600	0.810	0.215	KURU	--	KURU	0.740	0.335	0.153	0.180
Ortalama	0.669	1.22	0.815	0.810	0.620	0.454	--	7.27	1.61	0.794	0.256	0.226
LT/SN/Km2	3.22	5.89	3.93	3.90	2.99	2.19	--	35.0	7.75	3.82	1.24	1.09
AKIM mm.	8.64	15.3	10.5	10.5	7.22	5.85	--	93.8	20.1	10.2	3.31	2.82
MİL. M3	1.79	3.17	2.18	2.17	1.50	1.22	--	19.5	4.17	2.13	0.687	0.586

SU YILI (2006)

23. Çoruh Havzasi

D23A041 ESENDORUK TORTUMKALE

YERİ : ERZURUM ARTVİN YOLUNUN 55 KM SİNDEN SOLA AYRILAN YOLUN 3 KM SİNDEKİ TORTUMKALE KÖYÜNÜN CAMİSİNİN YANINDADIR.
41°28'19" Doğu - 40°20'36" Kuzey

YAĞIŞ ALANI : 282,00 km2 **YAKLAŞIK KOT** : 1425 m

GÖZLEM SÜRESİ : 01.10.1999 - 30.09.2006

ORTALAMA AKIMLAR : Gözlem süresinde 3.772 m3/sn. (7 Yıllık) 2006 Su yılında 3.795 m3/sn.

ANLIK EN ÇOK VE EN AZ AKIMLAR:

2006 Su yılında anlık ençok akım	:	22.6	m3/sn	08.05.2006
2006 Su yılında anlık enaz akım	:	0.640	m3/sn	17.01.2006
Gözlem süresinde anlık ençok akım	:	27.9	m3/sn	03.04.2001
Gözlem süresinde anlık enaz akım	:	0.640	m3/sn	17.01.2006

6. Anahtar Eğrisi (Seviyeler cm olarak)

Seviye	Akım	Seviye	Akım	Seviye	Akım	Seviye	Akım
5	0.019	20	1.2	130	36.6	280	128.
8	0.115	35	3.6	160	51.7	310	151.
11	0.286	50	7.0	190	68.7	320	159.
14	0.524	70	12.7	220	87.2	330	167.
17	0.819	100	23.4	250	107.	340	175.

Akımlar 01 Ekim 2005 'den 30 Eylül 2006' a kadar m3/sn olarak

Gün	Ekim	Kasım	Aralık	Ocak	Şubat	Mart	Nisan	Mayıs	Haziran	Temmuz	Ağustos	Eylül
01	1.91	3.39	1.91	3.18	1.23	1.00	3.60	9.60	9.60	4.70	2.07	1.75
02	1.91	2.76	1.91	3.18	1.23	1.10	3.82	12.7	9.95	5.26	2.23	1.75
03	1.91	2.55	2.07	3.18	1.23	1.00	4.04	12.7	10.3	5.82	2.55	1.75
04	1.91	2.39	2.07	2.97	0.900	1.10	3.60	12.7	9.25	6.10	2.23	1.75
05	1.91	2.55	2.07	3.18	0.900	1.00	3.39	12.3	8.90	5.54	2.07	1.91
06	1.91	2.55	2.07	3.18	0.900	1.00	3.18	13.2	8.55	4.98	1.91	2.07
07	1.91	2.39	1.91	3.39	0.900	1.00	3.18	14.9	9.60	4.70	1.75	1.91
08	1.75	2.55	1.91	1.75	0.900	1.00	3.39	17.1	8.20	4.48	1.75	1.91
09	1.75	2.39	1.91	1.62	0.900	1.23	4.98	18.0	7.50	4.26	1.75	2.07
10	1.75	2.23	1.91	1.49	0.900	1.10	5.82	17.6	6.94	4.04	1.75	1.91
11	1.75	2.23	1.91	1.23	0.900	1.00	6.38	16.2	6.38	3.82	1.75	1.91
12	1.75	2.07	1.91	1.23	0.900	1.00	6.38	15.8	5.82	3.60	1.75	2.07
13	1.75	2.07	1.75	1.23	0.900	1.00	6.94	15.8	5.54	3.39	1.62	2.07
14	1.75	1.91	1.75	1.23	0.900	1.10	7.50	15.8	5.26	3.18	1.62	2.07
15	1.91	1.91	1.91	1.23	0.900	1.91	9.25	14.4	4.70	2.97	1.62	2.07
16	1.91	1.91	1.91	1.10	0.900	1.91	13.6	13.6	4.48	3.18	1.62	2.07
17	2.97	1.91	1.91	0.800	0.900	1.91	12.7	14.0	4.26	2.97	1.62	2.23
18	2.23	1.91	1.91	1.10	1.36	1.91	11.4	14.0	4.26	2.97	1.62	2.23
19	2.55	1.91	1.91	1.10	1.36	1.91	11.0	12.7	4.04	2.97	1.75	2.23
20	2.55	1.91	1.91	1.10	1.00	1.91	10.7	11.4	3.82	2.97	1.91	2.07
21	2.39	1.91	1.91	1.10	0.900	1.91	11.9	11.4	3.60	2.76	2.23	2.07
22	2.23	1.91	1.75	1.10	0.900	1.75	12.7	11.4	3.39	2.55	2.76	2.07
23	2.23	1.75	1.91	1.10	1.00	1.91	12.3	11.4	3.39	2.55	2.76	2.39
24	2.07	1.75	1.91	1.10	1.00	2.07	14.9	11.4	3.18	2.23	2.23	2.55
25	2.07	1.91	1.91	1.10	0.900	2.55	14.9	11.0	3.18	2.23	2.07	2.39
26	2.07	1.91	1.75	1.10	0.900	2.76	12.3	11.0	3.18	2.23	2.07	2.39
27	1.91	1.91	1.75	1.10	0.900	2.55	10.7	11.0	4.04	2.23	2.07	2.23
28	2.07	1.91	2.39	0.800	1.00	2.55	9.25	11.0	5.54	2.39	1.91	2.23
29	2.39	1.91	2.55	1.23	-----	2.55	8.20	10.3	5.54	2.39	1.75	2.23
30	2.39	2.07	3.18	1.10	-----	2.76	9.25	9.95	4.98	2.23	1.62	2.39
31	2.97	-----	3.18	1.00	-----	2.97	-----	9.60	-----	2.23	1.75	-----
Maks.	4.26	3.82	5.54	5.82	1.36	3.60	18.5	22.6	13.6	7.22	3.18	2.97
Min.	1.62	1.62	1.62	0.640	0.900	1.00	3.18	8.90	3.18	1.91	1.49	1.62
Ortalama	2.08	2.15	2.02	1.62	0.982	1.69	8.38	13.0	5.91	3.48	1.94	2.09
LT/SN/Km2	7.38	7.62	7.17	5.75	3.48	6.00	29.7	46.2	21.0	12.3	6.88	7.42
AKIM mm.	19.8	19.7	19.2	15.4	8.43	16.1	77.0	124.	54.3	33.1	18.4	19.2
MİL. M3	5.58	5.57	5.42	4.35	2.38	4.53	21.7	34.9	15.3	9.32	5.20	5.42

SU YILI (2006) YILLIK TOPLAM AKIM 119.67 MİLYON M3 424 MM. 13.5 LT/SN/Km2

23. Çoruh Havzasi

D23A042 GÖKTEPE D. KALEBOYNU

YERİ : ERZURUM ARTVİN KARAYOLUNUN 65 KM SİNDE ŞENYURT NAHİYESİNİN 15 KM SİNDEKİ KALEBOYNU KÖYÜNDEDİR.
41°21'44" Doğu - 40°25'5" Kuzey

YAĞIŞ ALANI : 88,50 km2 YAKLAŞIK KOT : 1824 m

GÖZLEM SÜRESİ : 01.10.1999 - 30.09.2006

ORTALAMA AKIMLAR : Gözlem süresinde 1.440 m3/sn. (6 Yıllık) 2006 Su yılında ---- m3/sn.

ANLIK EN ÇOK VE EN AZ AKIMLAR:

2006 Su yılında anlık ençok akım : ----- m3/sn

2006 Su yılında anlık enaz akım : ----- m3/sn

Gözlem süresinde anlık ençok akım : 10.9 m3/sn 28.05.2004

Gözlem süresinde anlık enaz akım : 0.195 m3/sn 30.10.2003

3. Anahtar Eğrisi (Seviyeler cm olarak)

Seviye	Akım	Seviye	Akım
66	0.096	100	4.2
68	0.120	110	7.1
70	0.150	120	10.4
80	0.680	130	14.1
90	1.9		

Akımlar 01 Ekim 2005 'den 30 Eylül 2006' a kadar m3/sn olarak

Gün	Ekim	Kasım	Aralık	Ocak	Şubat	Mart	Nisan	Mayıs	Haziran	Temmuz	Ağustos	Eylül
01	0.908	0.820	0.588	0.530	0.588	0.588	0.908	-----	-----	-----	0.996	0.588
02	0.820	0.704	0.588	0.530	0.484	0.588	0.908	-----	-----	-----	0.996	0.588
03	0.820	0.762	0.646	0.530	0.530	0.588	0.908	-----	-----	-----	0.820	0.530
04	0.820	0.704	0.646	0.530	0.588	0.588	0.820	-----	-----	-----	0.820	0.588
05	0.820	0.704	0.646	0.484	0.530	0.588	0.762	-----	-----	-----	0.820	0.646
06	0.762	0.704	0.646	0.484	0.530	0.530	0.762	-----	-----	-----	0.762	0.646
07	0.762	0.704	0.588	0.588	0.530	0.588	0.762	-----	-----	-----	0.704	0.588
08	0.762	0.704	0.588	0.588	0.530	0.588	0.996	-----	-----	-----	0.762	0.646
09	0.762	0.646	0.588	0.588	0.530	0.646	1.44	-----	-----	-----	0.704	0.588
10	0.762	0.646	0.588	0.588	0.530	0.588	1.70	-----	-----	-----	0.646	0.646
11	0.762	0.646	0.588	0.530	0.530	0.588	2.30	-----	-----	-----	0.646	0.646
12	0.762	0.646	0.588	0.530	0.530	0.588	2.60	-----	-----	-----	0.646	0.646
13	0.762	0.646	0.588	0.530	0.530	0.588	3.05	-----	-----	-----	0.646	0.704
14	0.762	0.588	0.588	0.530	0.530	0.588	3.90	-----	-----	-----	0.646	0.704
15	0.762	0.588	0.588	0.530	0.588	0.588	4.60	-----	-----	-----	0.646	0.704
16	0.762	0.588	0.588	0.588	0.530	0.588	6.27	-----	-----	-----	0.646	0.646
17	1.17	0.588	0.530	0.646	0.588	0.588	5.17	-----	-----	-----	0.646	0.646
18	0.820	0.588	0.646	0.646	0.588	0.588	4.78	-----	-----	-----	0.646	0.646
19	1.17	0.588	0.588	0.646	0.530	0.588	4.43	-----	-----	-----	0.646	0.646
20	1.08	0.588	0.588	0.646	0.438	0.588	4.43	-----	-----	-----	0.762	0.646
21	0.908	0.588	0.588	0.646	0.530	0.588	4.78	-----	-----	-----	0.820	0.646
22	0.908	0.588	0.588	0.646	0.530	0.588	4.78	-----	-----	-----	0.820	0.646
23	0.820	0.588	0.588	0.646	0.530	0.588	4.78	-----	-----	-----	0.762	0.762
24	0.762	0.588	0.588	0.484	0.530	0.646	5.61	-----	-----	-----	0.704	0.762
25	0.762	0.588	0.588	0.438	0.530	0.704	5.39	-----	-----	-----	0.704	0.704
26	0.820	0.588	0.530	0.530	0.530	0.704	4.60	-----	-----	-----	0.646	0.704
27	0.762	0.588	0.530	0.530	0.588	0.762	3.90	-----	-----	-----	0.646	0.704
28	0.762	0.646	0.530	0.530	0.530	0.704	3.55	-----	-----	-----	0.646	0.704
29	0.762	0.588	0.530	0.588	-----	0.762	3.05	-----	-----	-----	0.646	0.588
30	0.762	0.646	0.530	0.588	-----	0.762	3.20	-----	-----	-----	0.646	0.646
31	0.820	-----	0.530	0.588	-----	0.762	-----	-----	-----	-----	0.588	-----
Maks.	1.52	1.08	1.08	0.646	0.762	0.908	6.71	--	--	--	1.52	0.996
Min.	0.588	0.530	0.484	0.392	0.346	0.530	0.762	--	--	--	0.588	0.530
Ortalama	0.828	0.638	0.584	0.564	0.537	0.624	3.17	--	--	--	0.717	0.652
LT/SN/Km2	9.35	7.21	6.60	6.37	6.07	7.05	35.8	--	--	--	8.10	7.36
AKIM mm.	25.0	18.7	17.7	17.1	14.7	18.9	92.9	--	--	--	21.7	19.1
MİL. M3	2.22	1.65	1.56	1.51	1.30	1.67	8.22	--	--	--	1.92	1.69

SU YILI (2006)

24

ARAS HAVZASI

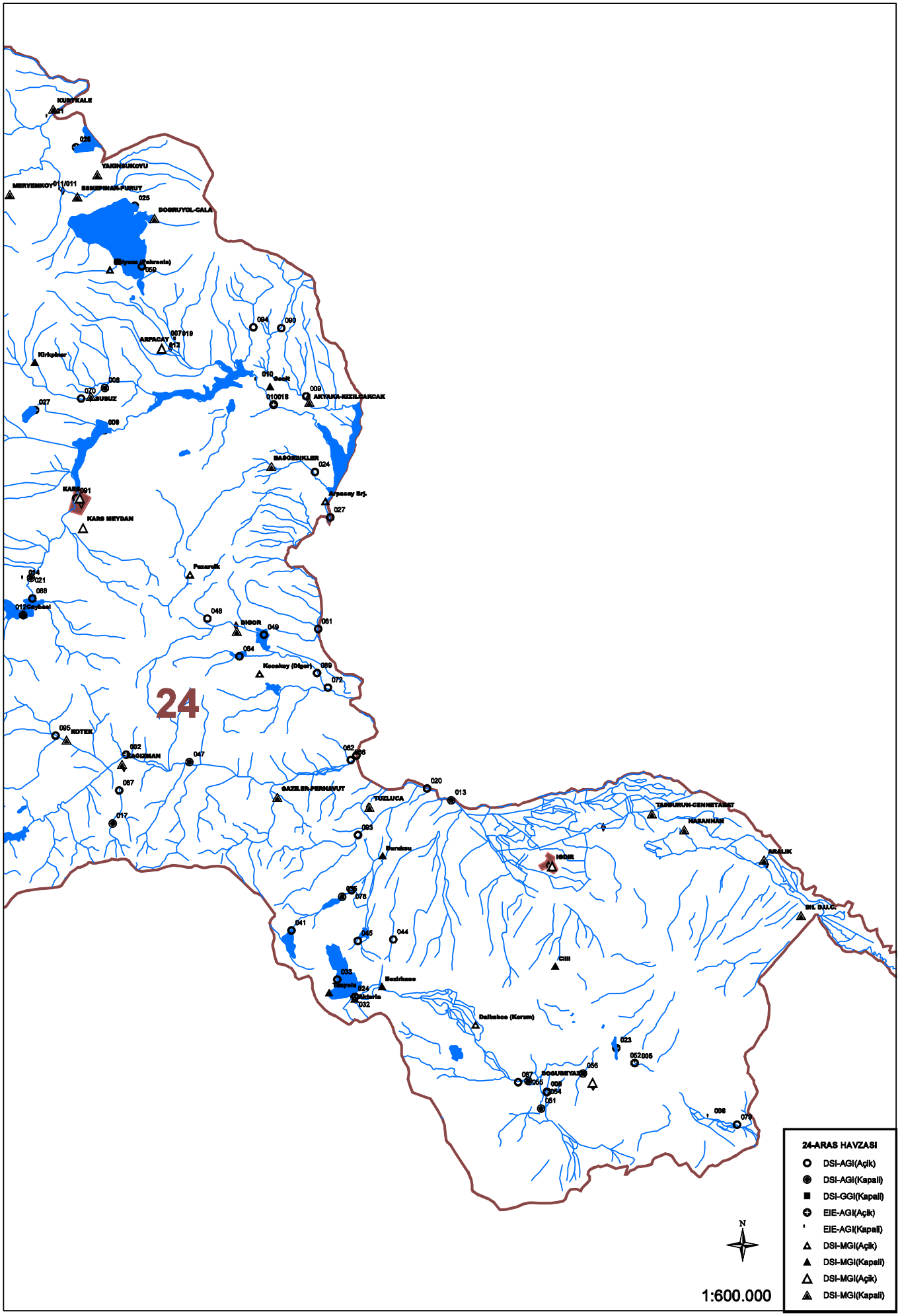
24
KURUKALE
YAKINBUKOYU
MERYEMKOY
011/011
ESMEPINAR-PURUT
025
DOGRUYOL-CALA
Ilyuzu (Sakrenis)
059
ARPACAY
007/019
012
Kirkpinar
008
070
SUSUZ
027
009
AKYAKA-KIZILDAMCAK
010
Sebik
010/018
009
BAGCEDIKLER
024
Arpacay Brj.
027
KARS
091
KARS MEYDAN
Pazarcik
014
021
088
012
Crystal
048
IGDIR
049
061
064
Kocakoy (Digor)
069
072
095
KOTEK
002
BAGISMAN
047
062
068
067
017
GAZELER-PERNAVUT
020
013
TUZLUCA
TASDURUN-CENNETABAT
HASANHAN
093
Nurakoy
IGDIR
ARALIK
075
078
BIL D.U.C.
041
045
044
CIHI
033
Hayeli
024
Ikizarta
032
Bezirhane
Dalbahce (Korum)
023
052
006
056
057
055
008
054
051
006
079
24-ARAS HAVZASI
DSI-AGI(Açik)
DSI-AGI(Kapali)
DSI-GGI(Kapali)
EIE-AGI(Açik)
EIE-AGI(Kapali)
DSI-MGI(Açik)
DSI-MGI(Kapali)
DSI-MGI(Açik)
DSI-MGI(Kapali)
N
1:600.000

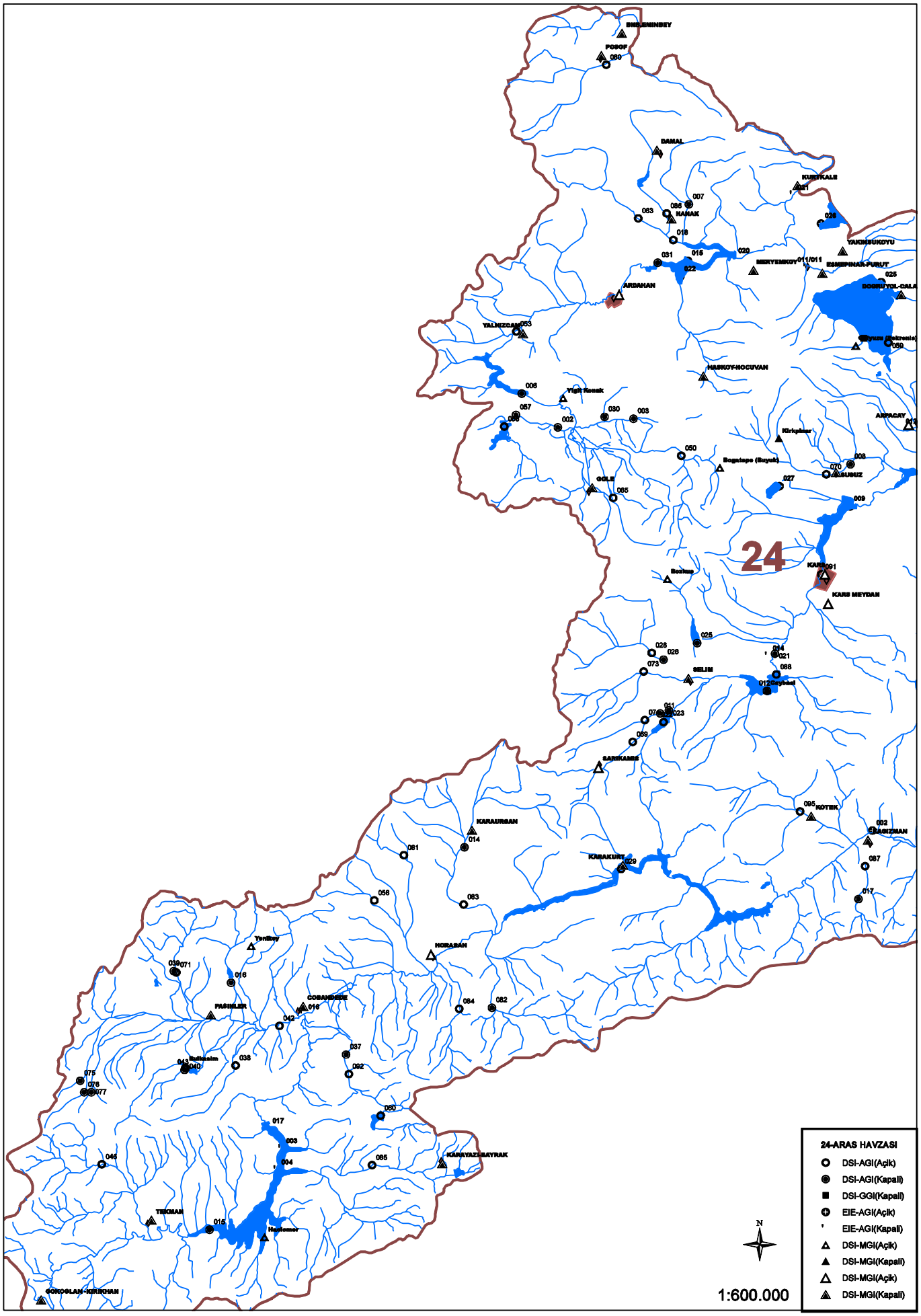
24
24-ARAS HAVZASI
DSI-AGI(Açik)
DSI-AGI(Kapali)
DSI-GGI(Kapali)
EIE-AGI(Açik)
EIE-AGI(Kapali)
DSI-MGI(Açik)
DSI-MGI(Kapali)
DSI-MGI(Açik)
DSI-MGI(Kapali)
N
1:600.000
DAMAL
HAMAK
ARDAHAN
YALNIZCAM
HASKOY-HOCUVAN
ARPACAY
GOLE
SELIM
KARS MEYDAN
SARIKAMIS
KOTEK
KARAURGAN
KARAKURT
HORASAN
TEKMAN
KANYAZI-BAYRAK
GOKOGLAN-KIRIKHAN

24. Aras Havzasi

D24A009 KARAHAN ÇAYI AKYAKA

YERİ : **KARS İLİ AKYAKA ILÇESI JANDARMA BITIŞIĞINDEKİ KÖPRÜDEDIR.**
43°37'12" Doğu - 40°44'6" Kuzey

YAĞIŞ ALANI : **366,00 km2** **YAKLAŞIK KOT : 1480 m**

GÖZLEM SÜRESİ : **07.10.1959 - 30.09.2006**

ORTALAMA AKIMLAR : **Gözlem süresinde 2.044 m3/sn. (7 Yıllık) 2006 Su yılında 3.513 m3/sn.**

ANLIK EN ÇOK VE EN AZ AKIMLAR:

2006 Su yılında anlık ençok akım	**:**	**60.4**	**m3/sn**	**11.04.2006**
2006 Su yılında anlık enaz akım	**:**	**0.200**	**m3/sn**	**04.03.2006**
Gözlem süresinde anlık ençok akım	**:**	**60.4**	**m3/sn**	**11.04.2006**
Gözlem süresinde anlık enaz akım	**:**	**0.200**	**m3/sn**	**04.03.2006**

Akımlar 01 Ekim 2005 'den 30 Eylül 2006' a kadar m3/sn olarak

Gün	Ekim	Kasım	Aralık	Ocak	Şubat	Mart	Nisan	Mayıs	Haziran	Temmuz	Ağustos	Eylül
01	1.45	3.29	1.77	2.68	2.68	2.68	3.19	6.62	2.78	1.77	1.67	1.31
02	1.45	3.60	1.77	2.68	2.68	2.68	7.43	24.5	2.78	1.77	1.87	1.31
03	1.23	3.09	1.67	2.68	2.68	2.68	11.5	23.5	2.78	1.97	1.67	1.31
04	1.23	2.58	1.77	2.68	2.68	2.68	17.1	20.3	2.68	1.97	1.52	1.31
05	1.23	2.48	1.77	2.68	2.68	2.68	3.19	8.48	2.78	1.87	1.52	1.38
06	1.23	2.78	1.67	2.68	2.68	2.68	1.77	7.22	2.99	1.87	1.52	1.31
07	1.16	2.78	1.60	2.68	2.68	2.68	6.08	27.0	2.88	1.67	1.38	1.45
08	1.16	2.78	1.60	2.68	2.68	2.68	15.6	9.59	2.48	1.60	1.38	1.16
09	1.16	2.48	1.52	2.68	2.68	2.68	22.8	12.6	2.48	1.97	1.38	1.01
10	1.16	2.18	1.52	2.68	2.68	2.68	33.6	17.4	2.28	1.60	1.45	1.52
11	1.16	1.97	1.52	2.68	2.68	2.68	60.4	6.80	2.18	2.18	1.52	1.52
12	1.16	2.07	1.45	2.68	2.68	2.68	42.9	4.61	2.07	1.87	1.52	1.87
13	1.16	1.77	0.898	2.68	2.68	2.68	11.8	3.96	1.97	1.67	1.45	1.60
14	1.09	1.87	0.855	2.68	2.68	2.68	24.9	3.60	1.97	1.52	1.31	1.60
15	1.16	1.77	0.813	2.68	2.68	2.68	22.8	3.19	2.07	1.52	1.38	1.67
16	1.16	1.67	0.898	2.68	2.68	2.68	20.0	1.97	1.97	1.67	1.31	1.77
17	1.38	1.67	0.940	2.68	2.68	2.68	12.3	2.28	1.87	1.52	1.23	1.52
18	1.97	1.67	1.01	2.68	2.68	2.68	9.82	3.09	1.87	1.38	1.38	1.60
19	1.87	1.60	0.940	2.68	2.68	2.68	6.26	2.18	1.87	1.38	1.52	1.45
20	1.77	1.67	1.97	2.68	2.68	2.68	4.74	1.67	2.07	1.38	1.60	1.38
21	1.67	1.67	2.68	2.68	2.68	2.68	6.62	1.38	1.97	1.31	1.45	1.31
22	1.67	1.87	2.68	2.68	2.68	2.68	8.48	1.60	1.87	1.31	1.31	1.38
23	1.52	1.67	2.68	2.68	2.68	2.68	6.62	1.31	1.97	1.23	1.38	1.38
24	1.45	1.52	2.68	2.68	2.68	2.68	30.8	1.09	1.87	1.23	1.31	1.45
25	1.45	1.45	2.68	2.68	2.68	2.68	34.4	3.50	1.52	1.23	1.45	1.38
26	1.38	1.60	2.68	2.68	2.68	2.68	12.0	3.19	1.45	1.23	1.31	1.45
27	1.38	1.67	2.68	2.68	2.68	2.68	6.44	3.09	2.38	1.31	1.52	1.31
28	1.38	1.67	2.68	2.68	2.68	2.68	4.87	3.19	2.18	1.38	1.31	1.38
29	1.60	1.67	2.68	2.68	-----	2.68	3.70	2.88	2.07	1.52	1.31	1.38
30	1.97	1.77	2.68	2.68	-----	1.60	7.64	2.78	2.07	1.45	1.23	1.38
31	2.38	-----	2.68	2.68	-----	1.38	-----	2.78	-----	1.60	1.31	-----
Maks.	2.78	4.09	2.99	2.68	2.68	2.68	60.4	34.0	2.99	3.09	1.87	1.87
Min.	0.898	0.685	0.770	2.68	2.68	0.200	1.77	1.09	1.45	1.16	1.23	1.01
Ortalama	1.43	2.08	1.85	2.68	2.68	2.60	15.3	7.01	2.21	1.58	1.43	1.43
LT/SN/Km2	3.89	5.68	5.06	7.32	7.32	7.11	41.9	19.2	6.03	4.31	3.92	3.90
AKIM mm.	10.4	14.7	13.6	19.6	17.7	19.1	109.	51.3	15.6	11.6	10.5	10.1
MİL. M3	3.82	5.39	4.96	7.18	6.48	6.97	39.7	18.8	5.72	4.23	3.84	3.70

SU YILI (2006) YILLIK TOPLAM AKIM 110.79 MİLYON M3 303 MM. 9.6 LT/SN/Km2

24. Aras Havzasi

D24A010 KARS Ç. SAHNALAR

YERİ : **KARS İLI AKYAKA ILÇESI ŞAHNALAR KÖYÜNÜN 300 M. MANSABINDADIR.**
43°33'10" Doğu - 40°44'7" Kuzey

YAĞIŞ ALANI : **4793,00 km2** **YAKLAŞIK KOT : 1510 m**

GÖZLEM SÜRESİ : **01.10.1961 - 30.09.2006**

ORTALAMA AKIMLAR : **Gözlem süresinde 19.032 m3/sn. (7 Yıllık) 2006 Su yılında 28.694 m3/sn.**

ANLIK EN ÇOK VE EN AZ AKIMLAR:

2006 Su yılında anlık ençok akım	:	**152.**	**m3/sn**	**25.04.2006**
2006 Su yılında anlık enaz akım	:	**7.44**	**m3/sn**	**17.08.2006**
Gözlem süresinde anlık ençok akım	:	**206.**	**m3/sn**	**31.05.2004**
Gözlem süresinde anlık enaz akım	:	**1.85**	**m3/sn**	**22.08.2000**

Akımlar 01 Ekim 2005 'den 30 Eylül 2006' a kadar m3/sn olarak

Gün	Ekim	Kasım	Aralık	Ocak	Şubat	Mart	Nisan	Mayıs	Haziran	Temmuz	Ağustos	Eylül
01	16.0	25.9	17.8	22.7	22.7	22.7	104.	87.4	23.3	16.9	9.94	9.28
02	16.0	27.9	17.8	22.7	22.7	22.7	120.	90.9	22.7	18.2	11.0	9.28
03	14.7	24.6	17.3	22.7	22.7	22.7	125.	94.6	24.0	27.9	11.0	9.28
04	14.7	21.5	17.8	22.7	22.7	23.3	128.	99.8	24.0	24.0	11.3	9.28
05	14.7	21.1	17.8	22.7	22.7	22.0	95.9	87.4	22.0	22.7	10.6	8.96
06	14.7	22.7	17.3	22.7	22.7	22.0	84.0	95.9	21.1	21.1	9.94	8.96
07	14.3	22.7	16.9	22.7	22.7	22.7	73.6	101.	20.6	23.3	9.60	8.96
08	14.3	22.7	16.9	22.7	22.7	27.9	63.3	88.6	21.1	19.2	9.28	10.3
09	14.3	21.1	16.4	22.7	22.7	37.1	84.0	98.5	19.2	17.8	9.28	10.3
10	14.3	19.7	16.4	22.7	22.7	33.7	110.	81.7	19.2	16.0	8.64	9.60
11	14.3	18.7	16.4	22.7	22.7	31.1	106.	72.5	19.2	16.4	8.32	9.60
12	14.3	19.2	16.0	22.7	22.7	30.5	102.	64.3	18.7	14.7	8.00	10.6
13	14.3	17.8	12.7	22.7	22.7	31.8	92.0	63.3	18.7	13.0	7.72	10.6
14	13.9	18.2	12.3	22.7	22.7	35.0	86.3	61.4	13.4	12.7	7.72	10.6
15	14.3	17.8	12.0	22.7	22.7	33.7	85.1	63.3	12.0	12.7	7.72	11.0
16	14.3	17.3	12.7	22.7	22.7	33.7	87.4	57.6	11.3	13.0	7.44	11.3
17	15.6	17.3	13.9	22.7	22.7	33.7	88.6	52.9	11.0	12.7	7.44	11.6
18	18.7	17.3	13.4	22.7	22.7	33.7	84.0	54.8	10.6	12.3	7.72	12.0
19	18.2	16.9	13.0	22.7	22.7	29.8	71.3	51.9	10.3	12.0	8.32	13.0
20	17.8	17.3	17.8	22.7	22.7	27.2	65.2	47.6	10.6	12.0	9.94	13.0
21	17.3	17.3	22.7	22.7	22.7	26.6	69.0	50.0	11.6	11.3	7.72	12.7
22	17.3	18.2	22.7	22.7	22.7	30.5	86.3	51.9	11.6	11.6	10.6	13.0
23	16.4	17.3	22.7	22.7	22.7	37.8	80.5	42.0	12.0	11.3	10.6	13.0
24	16.0	16.4	22.7	22.7	22.7	49.2	118.	41.3	13.0	11.3	9.94	13.0
25	16.0	16.0	22.7	22.7	22.7	65.2	152.	34.4	16.0	11.0	11.6	13.0
26	15.6	16.9	22.7	22.7	22.7	61.4	145.	32.4	13.9	9.28	10.3	13.0
27	15.6	17.3	22.7	22.7	22.7	57.6	104.	31.1	13.0	10.6	10.6	13.9
28	15.6	17.3	22.7	22.7	22.7	62.4	82.8	31.1	13.4	10.6	10.6	13.4
29	16.9	17.3	22.7	22.7	-----	63.3	68.1	29.8	18.2	10.6	10.3	13.4
30	18.7	17.8	22.7	22.7	-----	70.2	79.4	27.9	16.4	10.6	9.94	13.4
31	20.6	-----	22.7	22.7	-----	69.0	-----	25.3	-----	8.32	9.28	-----
Maks.	22.7	30.5	22.7	22.7	22.7	74.8	152.	101.	24.6	27.9	11.6	13.9
Min.	12.7	16.0	11.6	22.7	22.7	22.0	63.3	24.6	10.3	8.32	7.44	8.96
Ortalama	15.8	19.3	18.1	22.7	22.7	37.7	94.7	61.7	16.4	14.7	9.43	11.3
LT/SN/Km2	3.30	4.03	3.78	4.74	4.74	7.88	19.8	12.9	3.42	3.06	1.97	2.36
AKIM mm.	8.83	10.4	10.1	12.7	11.5	21.1	51.2	34.5	8.87	8.20	5.27	6.12
MİL. M3	42.3	50.1	48.6	60.8	54.9	101.	245.	165.	42.5	39.3	25.3	29.3

SU YILI (2006) YILLIK TOPLAM AKIM 904.10 MİLYON M3 189 MM. 6.0 LT/SN/Km2

24. Aras Havzasi

D24A018 KANTARLI ÇAYI Çayagzi

YERİ : **ARDAHAN İLI HANAK ILÇESI ÇAYAĞZI KÖYÜNDE YER ALIR.**
42°50'54" Doğu - 41°11'52" Kuzey

YAĞIŞ ALANI : **502,00 km2** **YAKLAŞIK KOT : 1775 m**

GÖZLEM SÜRESİ : **01.11.1961 - 30.09.2006**

ORTALAMA AKIMLAR : **Gözlem süresinde 5.396 m3/sn. (38 Yıllık) 2006 Su yılında 5.521 m3/sn.**

ANLIK EN ÇOK VE EN AZ AKIMLAR:

2006 Su yılında anlık ençok akım	**:**	**39.0**	**m3/sn**	**14.04.2006**
2006 Su yılında anlık enaz akım	**:**	**0.480**	**m3/sn**	**03.12.2005**
Gözlem süresinde anlık ençok akım	**:**	**130.**	**m3/sn**	**30.04.1969**
Gözlem süresinde anlık enaz akım	**:**	**0.018**	**m3/sn**	**15.12.2000**

Akımlar 01 Ekim 2005 'den 30 Eylül 2006' a kadar m3/sn olarak

Gün	Ekim	Kasım	Aralık	Ocak	Şubat	Mart	Nisan	Mayıs	Haziran	Temmuz	Ağustos	Eylül
01	2.00	7.76	2.40	2.40	2.40	2.40	3.35	16.2	9.80	5.30	3.20	2.80
02	1.55	7.76	1.55	2.40	2.40	2.40	9.80	16.2	9.80	5.30	3.60	2.43
03	1.55	6.40	1.55	2.40	2.40	2.40	20.1	14.7	9.80	6.40	3.20	2.43
04	2.00	6.40	2.00	2.40	2.40	2.40	26.2	14.7	9.80	5.90	3.60	2.43
05	2.00	6.40	1.55	2.40	2.40	2.40	20.1	14.0	9.80	5.30	3.20	2.43
06	2.00	5.90	1.55	2.40	2.40	2.40	22.7	17.8	9.80	6.40	3.20	2.43
07	1.55	5.90	2.40	2.40	2.40	2.40	25.4	13.2	9.80	5.90	2.80	2.43
08	2.00	5.30	2.40	2.40	2.40	2.40	23.6	12.5	8.44	6.40	2.80	2.43
09	2.00	4.80	2.40	2.40	2.40	2.40	19.3	12.5	7.76	5.90	2.80	2.43
10	1.55	4.35	2.40	2.40	2.40	2.40	18.6	11.8	6.40	7.08	2.80	2.43
11	1.55	4.35	2.40	2.40	2.40	2.40	17.0	11.8	6.40	4.80	2.80	2.43
12	1.55	4.35	2.40	2.40	2.40	2.40	27.1	9.80	5.90	3.85	2.80	2.43
13	1.55	4.35	2.40	2.40	2.40	2.40	29.8	9.80	5.90	3.35	2.80	2.43
14	1.55	4.35	2.40	2.40	2.40	2.40	34.4	9.80	5.90	2.90	2.80	2.43
15	2.00	4.35	2.40	2.40	2.40	2.40	30.7	9.80	4.80	4.35	2.80	2.43
16	2.00	4.35	2.40	2.40	2.40	2.40	28.9	9.12	4.80	4.43	2.80	2.43
17	3.85	3.85	2.40	2.40	2.40	2.40	25.4	9.12	4.80	4.03	2.80	2.43
18	3.85	3.85	2.40	2.40	2.40	2.40	20.9	9.12	4.80	4.43	2.43	2.43
19	3.35	3.85	2.40	2.40	2.40	2.40	20.9	9.12	4.80	4.03	2.80	2.08
20	3.85	3.35	2.40	2.40	2.40	2.40	22.7	8.44	4.80	3.60	3.60	2.08
21	3.35	3.35	2.40	2.40	2.40	2.40	24.5	9.12	4.80	3.60	3.60	2.08
22	3.35	3.35	2.40	2.40	2.40	2.40	28.9	10.5	4.80	3.60	4.43	2.08
23	2.90	2.40	2.40	2.40	2.40	2.40	21.8	10.5	4.80	3.60	3.60	2.43
24	2.90	2.90	2.40	2.40	2.40	2.40	20.1	9.80	4.80	3.60	3.20	2.43
25	2.40	3.85	2.40	2.40	2.40	5.30	21.8	9.80	4.80	3.60	3.20	2.43
26	2.90	2.90	2.40	2.40	2.40	6.40	20.9	9.12	5.30	3.20	3.20	2.43
27	2.90	2.90	2.40	2.40	2.40	5.30	20.9	8.44	4.80	3.20	3.20	2.43
28	2.90	2.90	2.40	2.40	2.40	3.85	19.3	9.12	4.80	3.20	2.80	2.43
29	3.35	2.90	2.40	2.40	-----	3.35	19.3	8.44	5.90	3.20	2.80	2.43
30	3.85	2.90	2.40	2.40	-----	3.35	19.3	8.44	5.30	3.20	2.80	2.43
31	4.35	-----	2.40	2.40	-----	3.35	-----	9.12	-----	3.20	2.80	-----
Maks.	6.40	8.44	2.40	2.40	2.40	13.2	39.0	21.8	12.5	7.08	6.21	2.80
Min.	1.55	2.40	0.480	2.40	2.40	2.40	3.35	8.44	4.80	2.90	2.43	2.08
Ortalama	2.53	4.41	2.28	2.40	2.40	2.85	22.1	11.0	6.47	4.41	3.07	2.40
LT/SN/Km2	5.04	8.79	4.54	4.78	4.78	5.69	44.1	22.0	12.9	8.79	6.12	4.77
AKIM mm.	13.5	22.8	12.2	12.8	11.6	15.2	114.	58.8	33.4	23.6	16.4	12.4
MİL. M3	6.78	11.4	6.10	6.43	5.81	7.65	57.3	29.5	16.8	11.8	8.23	6.21

SU YILI (2006) YILLIK TOPLAM AKIM 174.01 MİLYON M3 347 MM. 11.0 LT/SN/Km2

24. Aras Havzasi

D24A029 ARAS N. KARAKURT

YERİ : **SARIKAMIŞA 32 KM. MESAFEDEKİ KARAKURT NAHİYESİNDE ERZURUM YOLU ÜZERİNDE ÇIKIŞTADIR**

42°36'0" Doğu - 40°9'0" Kuzey

YAĞIŞ ALANI : **7086,00 km2** **YAKLAŞIK KOT : 1443 m**

GÖZLEM SÜRESİ : **22.03.1966 - 30.09.2006**

ORTALAMA AKIMLAR : **Gözlem süresinde 44.121 m3/sn. (35 Yıllık) 2006 Su yılında 49.228 m3/sn.**

ANLIK EN ÇOK VE EN AZ AKIMLAR:

2006 Su yılında anlık ençok akım	:	**560.**	**m3/sn**	**20.05.2006**
2006 Su yılında anlık enaz akım	:	**7.97**	**m3/sn**	**14.10.2005**
Gözlem süresinde anlık ençok akım	:	**1033**	**m3/sn**	**28.04.1997**
Gözlem süresinde anlık enaz akım	:	**0.100**	**m3/sn**	**23.04.1977**

Akımlar 01 Ekim 2005 'den 30 Eylül 2006' a kadar m3/sn olarak

Gün	Ekim	Kasım	Aralık	Ocak	Şubat	Mart	Nisan	Mayıs	Haziran	Temmuz	Ağustos	Eylül
01	9.14	45.7	27.0	27.0	27.0	40.5	32.8	251.	52.7	13.6	13.6	12.9
02	9.14	44.4	27.0	27.0	27.0	35.3	54.8	328.	51.4	13.6	13.6	12.9
03	9.14	35.3	27.0	27.0	27.0	29.2	79.2	346.	54.0	23.8	13.6	12.9
04	9.14	31.6	27.0	27.0	27.0	30.4	89.1	386.	51.4	24.9	13.6	12.9
05	9.14	30.4	27.0	27.0	27.0	30.4	75.9	386.	51.4	24.9	13.6	12.9
06	9.14	30.4	27.0	27.0	27.0	29.2	56.3	428.	51.4	24.9	13.6	12.9
07	8.56	29.2	25.9	27.0	27.0	29.2	54.8	431.	50.2	24.9	13.6	12.9
08	8.56	29.2	25.9	27.0	27.0	29.2	69.2	428.	50.2	24.9	13.6	12.9
09	8.56	29.2	25.9	27.0	27.0	31.6	91.1	477.	50.2	24.9	13.6	12.9
10	8.56	29.2	25.9	27.0	27.0	32.8	110.	480.	50.2	24.9	13.6	12.9
11	8.56	28.0	25.9	27.0	27.0	32.8	139.	476.	50.2	24.9	13.6	12.9
12	8.56	28.0	25.9	27.0	27.0	32.8	155.	382.	50.2	24.9	13.6	12.9
13	8.56	28.0	25.9	27.0	27.0	32.8	143.	318.	50.2	24.9	13.6	12.9
14	7.97	28.0	25.9	27.0	27.0	32.8	132.	240.	50.2	24.9	13.6	12.3
15	7.97	28.0	25.9	27.0	27.0	32.8	153.	193.	48.9	24.9	13.6	12.3
16	7.97	28.0	25.9	27.0	27.0	32.8	167.	163.	48.9	24.9	13.6	12.3
17	10.3	27.0	25.9	27.0	27.0	32.8	192.	160.	48.9	24.9	13.6	12.3
18	19.2	27.0	25.9	27.0	27.0	32.8	177.	123.	48.9	24.9	13.6	12.3
19	15.9	27.0	25.9	27.0	27.0	32.8	153.	121.	20.1	24.9	13.6	12.3
20	14.3	27.0	25.9	27.0	27.0	32.8	121.	119.	17.5	14.2	13.6	12.3
21	14.3	27.0	19.2	27.0	27.0	32.8	108.	114.	16.7	14.2	13.6	9.14
22	13.6	27.0	16.7	27.0	27.0	32.8	108.	114.	13.6	14.2	13.6	9.14
23	12.9	27.0	27.0	27.0	27.0	32.8	106.	112.	13.6	13.6	13.6	9.14
24	12.9	27.0	27.0	27.0	27.0	32.8	110.	97.0	13.6	13.6	12.9	9.14
25	16.7	27.0	27.0	27.0	27.0	32.8	101.	90.5	13.6	13.6	12.9	9.14
26	20.1	27.0	27.0	27.0	27.0	32.8	97.0	81.8	13.6	13.6	12.9	9.14
27	20.1	27.0	27.0	27.0	27.0	32.8	162.	73.0	13.6	13.6	12.9	9.14
28	20.1	27.0	27.0	27.0	27.0	32.8	192.	63.1	13.6	13.6	12.9	9.14
29	21.0	27.0	27.0	27.0	-----	32.8	224.	58.2	13.6	13.6	12.9	9.14
30	23.8	27.0	27.0	27.0	-----	32.8	215.	56.5	13.6	13.6	12.9	9.14
31	30.4	-----	27.0	27.0	-----	32.8	-----	54.0	-----	13.6	12.9	-----
Maks.	37.9	51.7	27.0	27.0	27.0	41.8	251.	560.	54.0	25.9	13.6	12.9
Min.	7.97	27.0	16.7	27.0	27.0	29.2	32.8	54.0	13.6	13.6	12.9	9.14
Ortalama	13.0	29.4	25.9	27.0	27.0	32.5	122.	231.	36.2	19.8	13.4	11.5
LT/SN/Km2	1.84	4.14	3.66	3.81	3.81	4.58	17.3	32.5	5.11	2.80	1.89	1.62
AKIM mm.	4.93	10.7	9.80	10.2	9.22	12.3	44.7	87.2	13.2	7.49	5.07	4.21
MİL. M3	34.9	76.1	69.4	72.3	65.3	87.0	317.	618.	93.8	53.1	35.9	29.8

SU YILI (2006) YILLIK TOPLAM AKIM 1552.60 MİLYON M3 219 MM. 6.9 LT/SN/Km2

24. Aras Havzasi

D24A040 MASAT D. BULKASIM

YERİ : **PASİNLER İLÇESİNDEN SAĞA AYRILAN YSE YOLUNUN 9. KM SİNDEKİ BULKASIM KÖYÜNDEDİR. 41°37'5" Doğu - 39°53'54" Kuzey**

YAĞIŞ ALANI : **95,50 km2** **YAKLAŞIK KOT : 1778 m**

GÖZLEM SÜRESİ : **01.10.1982 - 30.09.2006**

ORTALAMA AKIMLAR : **Gözlem süresinde 1.406 m3/sn. (22 Yıllık) 2006 Su yılında 1.737 m3/sn.**

ANLIK EN ÇOK VE EN AZ AKIMLAR:

2006 Su yılında anlık ençok akım	**:**	**26.5**	**m3/sn**	**21.04.2006**
2006 Su yılında anlık enaz akım	**:**	**0.055**	**m3/sn**	**10.10.2005**
Gözlem süresinde anlık ençok akım	**:**	**68.0**	**m3/sn**	**18.05.1987**
Gözlem süresinde anlık enaz akım	**:**	**0.013**	**m3/sn**	**01.01.1971**

21. Anahtar Eğrisi (Seviyeler cm olarak)

Seviye	Akım	Seviye	Akım	Seviye	Akım	Seviye	Akım
1	0.014	11	0.393	25	1.6	90	20.0
3	0.054	13	0.522	35	3.0	110	29.5
5	0.113	15	0.657	45	4.8	120	35.0
7	0.189	17	0.821	55	7.0	130	40.5
9	0.281	19	0.990	70	11.7	140	46.0

Akımlar 01 Ekim 2005 'den 30 Eylül 2006' a kadar m3/sn olarak

Gün	Ekim	Kasım	Aralık	Ocak	Şubat	Mart	Nisan	Mayıs	Haziran	Temmuz	Ağustos	Eylül
01	0.067	1.24	0.265	0.200	0.200	0.055	1.35	10.8	3.04	0.860	0.370	0.250
02	0.067	0.894	0.265	0.200	0.200	0.055	1.74	11.5	3.04	0.790	0.415	0.250
03	0.067	0.780	0.265	0.200	0.200	0.067	1.87	11.5	3.04	1.42	0.415	0.250
04	0.067	0.700	0.395	0.200	0.200	0.120	1.61	12.6	2.70	1.12	0.370	0.288
05	0.067	0.700	0.460	0.200	0.200	0.160	1.24	12.2	2.54	1.12	0.370	0.288
06	0.055	0.620	0.395	0.200	0.200	0.160	1.12	14.5	2.54	0.948	0.330	0.288
07	0.055	0.620	0.395	0.200	0.200	0.200	1.24	15.2	2.54	0.860	0.330	0.288
08	0.055	0.620	0.330	0.200	0.200	0.200	1.35	16.4	2.22	0.720	0.330	0.330
09	0.055	0.540	0.330	0.200	0.200	0.265	2.42	15.6	2.06	0.720	0.288	0.330
10	0.055	0.460	0.330	0.200	0.200	0.200	3.47	13.3	1.78	0.650	0.288	0.330
11	0.055	0.395	0.330	0.200	0.200	0.200	4.33	11.1	1.78	0.650	0.250	0.288
12	0.055	0.395	0.330	0.200	0.200	0.200	4.56	11.1	1.66	0.580	0.250	0.330
13	0.055	0.395	0.330	0.200	0.200	0.200	6.17	11.1	1.66	0.510	0.250	0.330
14	0.055	0.330	0.460	0.200	0.200	0.200	8.32	9.76	1.42	0.510	0.250	0.370
15	0.055	0.330	0.540	0.200	0.200	0.200	10.5	8.40	1.21	0.510	0.250	0.370
16	0.055	0.330	0.265	0.200	0.200	0.200	16.3	7.86	1.12	0.510	0.250	0.370
17	1.24	0.330	0.200	0.200	0.160	0.200	12.2	8.40	1.04	0.415	0.250	0.370
18	0.330	0.265	0.265	0.200	0.200	0.200	10.0	7.59	1.04	0.415	0.288	0.370
19	0.265	0.265	0.265	0.200	0.200	0.200	8.64	6.24	0.948	0.415	0.330	0.370
20	0.330	0.265	0.200	0.200	0.200	0.200	10.0	5.97	0.948	0.370	0.288	0.370
21	0.200	0.265	0.200	0.200	0.160	0.200	18.7	5.70	0.860	0.370	0.288	0.370
22	0.200	0.200	0.265	0.200	0.160	0.200	14.8	5.70	0.790	0.370	0.370	0.370
23	0.160	0.265	0.265	0.200	0.160	0.200	12.9	5.70	0.790	0.370	0.330	0.460
24	0.160	0.395	0.265	0.200	0.200	0.265	18.1	5.49	0.720	0.370	0.370	0.460
25	0.120	0.330	0.200	0.200	0.200	0.460	14.1	5.27	0.650	0.370	0.330	0.415
26	0.120	0.265	0.200	0.200	0.200	0.460	10.1	4.84	0.650	0.370	0.288	0.415
27	0.120	0.265	0.200	0.200	0.200	0.460	8.40	4.41	0.720	0.370	0.288	0.415
28	0.120	0.265	0.200	0.200	0.120	0.540	7.32	4.20	0.720	0.370	0.288	0.415
29	0.160	0.265	0.200	0.200	-----	0.620	6.51	3.98	0.720	0.510	0.288	0.415
30	0.265	0.330	0.200	0.200	-----	0.700	9.08	3.55	0.720	0.460	0.288	0.415
31	1.12	-----	0.200	0.200	-----	1.01	-----	3.21	-----	0.415	0.250	-----
Maks.	5.71	1.61	0.700	0.200	0.200	1.35	26.5	21.5	3.55	13.7	0.790	0.510
Min.	0.055	0.120	0.067	0.200	0.067	0.055	1.12	3.04	0.650	0.330	0.220	0.250
Ortalama	0.189	0.444	0.291	0.200	0.191	0.277	7.61	8.81	1.52	0.595	0.308	0.353
LT/SN/Km2	1.98	4.65	3.04	2.09	2.00	2.90	79.7	92.3	15.9	6.23	3.22	3.69
AKIM mm.	5.29	12.0	8.15	5.61	4.85	7.78	207.	247.	41.3	16.7	8.63	9.57
MİL. M3	0.505	1.15	0.778	0.536	0.463	0.743	19.7	23.6	3.95	1.59	0.824	0.914

SU YILI (2006) YILLIK TOPLAM AKIM 54.75 MİLYON M3 573 MM. 18.2 LT/SN/Km2

24. Aras Havzasi

D24A046 MADRAK SUYU HASANAĞA KOMU

YERİ : **ERZURUM - PALANDÖKENDEN, TEKMAN YOLUNUN 35. KM SİNDEKİ HASANAĞA KOMUNDADIR.**
41°25'15" Doğu - 39°44'59" Kuzey

YAĞIŞ ALANI : **180,80 km2** **YAKLAŞIK KOT : 2000 m**

GÖZLEM SÜRESİ : **01.10.1975 - 30.09.2006**

ORTALAMA AKIMLAR : **Gözlem süresinde 2.535 m3/sn. (29 Yıllık) 2006 Su yılında 2.040 m3/sn.**

ANLIK EN ÇOK VE EN AZ AKIMLAR:

2006 Su yılında anlık ençok akım	**:**	**33.0**	**m3/sn**	**09.05.2006**
2006 Su yılında anlık enaz akım	**:**	**0.000**	**m3/sn**	**01.10.2005**
Gözlem süresinde anlık ençok akım	**:**	**76.0**	**m3/sn**	**10.04.1980**
Gözlem süresinde anlık enaz akım	**:**	**0.000**	**m3/sn**	**01.10.2005**

5. Anahtar Eğrisi (Seviyeler cm olarak)

Seviye	Akım	Seviye	Akım	Seviye	Akım	Seviye	Akım
24	0.010	34	0.076	60	1.4	160	32.0
26	0.016	36	0.110	80	4.5	170	36.8
28	0.025	38	0.150	100	9.4	180	42.0
30	0.037	40	0.200	120	15.8	190	47.5
32	0.054	50	0.600	140	23.4	200	53.0

Akımlar 01 Ekim 2005 'den 30 Eylül 2006' a kadar m3/sn olarak

Gün	Ekim	Kasım	Aralık	Ocak	Şubat	Mart	Nisan	Mayıs	Haziran	Temmuz	Ağustos	Eylül
01	KURU	KURU	KURU	KURU	KURU	KURU	KURU	16.9	6.80	2.48	1.04	0.450
02	KURU	KURU	KURU	KURU	KURU	KURU	KURU	17.3	6.57	2.62	0.950	0.400
03	KURU	KURU	KURU	KURU	KURU	KURU	KURU	16.5	6.11	2.75	0.950	0.450
04	KURU	KURU	KURU	KURU	KURU	KURU	KURU	17.7	5.42	2.35	0.880	0.450
05	KURU	KURU	KURU	KURU	KURU	KURU	KURU	17.3	5.19	2.21	0.740	0.500
06	KURU	KURU	KURU	KURU	KURU	KURU	KURU	19.9	4.96	1.94	0.740	0.500
07	KURU	KURU	KURU	KURU	KURU	KURU	KURU	20.7	4.96	1.81	0.670	0.500
08	KURU	KURU	KURU	KURU	KURU	KURU	KURU	23.4	4.15	1.67	0.670	0.500
09	KURU	KURU	KURU	KURU	KURU	KURU	KURU	23.4	3.80	1.67	0.670	0.500
10	KURU	KURU	KURU	KURU	KURU	KURU	KURU	21.5	3.63	1.67	0.670	0.500
11	KURU	KURU	KURU	KURU	KURU	KURU	KURU	18.8	3.45	1.40	0.600	0.500
12	KURU	KURU	KURU	KURU	KURU	KURU	KURU	19.9	3.10	1.31	0.600	0.500
13	KURU	KURU	KURU	KURU	KURU	KURU	KURU	21.1	3.10	1.31	0.600	0.500
14	KURU	KURU	KURU	KURU	KURU	KURU	KURU	19.5	2.93	1.31	0.550	0.500
15	KURU	KURU	KURU	KURU	KURU	KURU	KURU	17.3	2.62	1.31	0.550	0.500
16	KURU	KURU	KURU	KURU	KURU	KURU	KURU	15.5	2.48	1.31	0.550	0.500
17	KURU	KURU	KURU	KURU	KURU	KURU	KURU	12.3	2.48	1.31	0.550	0.500
18	KURU	KURU	KURU	KURU	KURU	KURU	KURU	10.6	2.35	1.31	0.600	0.500
19	KURU	KURU	KURU	KURU	KURU	KURU	KURU	9.69	2.35	1.31	0.600	0.500
20	KURU	KURU	KURU	KURU	KURU	KURU	KURU	9.40	2.21	1.31	0.600	0.500
21	KURU	KURU	KURU	KURU	KURU	KURU	KURU	9.40	2.08	1.31	0.600	0.500
22	KURU	KURU	KURU	KURU	KURU	KURU	KURU	9.40	1.94	1.31	0.600	0.500
23	KURU	KURU	KURU	KURU	KURU	KURU	KURU	9.40	1.94	1.31	0.670	0.670
24	KURU	KURU	KURU	KURU	KURU	KURU	28.0	9.14	1.67	1.31	0.600	0.600
25	KURU	KURU	KURU	KURU	KURU	KURU	22.2	9.98	1.67	1.31	0.550	0.670
26	KURU	KURU	KURU	KURU	KURU	KURU	15.8	9.40	1.81	1.31	0.550	0.670
27	KURU	KURU	KURU	KURU	KURU	KURU	12.7	9.14	1.81	1.31	0.600	0.670
28	KURU	KURU	KURU	KURU	KURU	KURU	11.7	8.88	1.81	1.22	0.550	0.670
29	KURU	KURU	KURU	KURU	-----	KURU	11.7	7.84	1.67	1.31	0.500	0.740
30	KURU	KURU	KURU	KURU	-----	KURU	15.5	7.32	1.67	1.22	0.500	0.670
31	KURU	-----	KURU	KURU	-----	KURU	-----	7.06	-----	1.13	0.500	-----
Maks.	KURU	KURU	KURU	KURU	KURU	KURU	28.0	33.0	8.36	17.3	3.80	1.04
Min.	KURU	KURU	KURU	KURU	KURU	KURU	KURU	6.57	1.40	1.13	0.450	0.320
Ortalama	KURU	KURU	KURU	KURU	KURU	KURU	3.92	14.4	3.22	1.56	0.645	0.537
LT/SN/Km2	0.000	0.000	0.000	0.000	0.000	0.000	21.7	79.5	17.8	8.64	3.57	2.97
AKIM mm.	0.000	0.000	0.000	0.000	0.000	0.000	56.2	213.	46.2	23.1	9.56	7.70
MİL. M3	0.000	0.000	0.000	0.000	0.000	0.000	10.2	38.5	8.36	4.18	1.73	1.39

SU YILI (2006) YILLIK TOPLAM AKIM 64.36 MİLYON M3 356 MM. 11.3 LT/SN/Km2

24. Aras Havzasi

D24A048 DİGOR S. GÜLHAYRAN

YERİ : **KARS DİGOR YOLU ÜZERINDE GÜLHAYRAN KÖYÜNDEDIR.**
43°20'19" Doğu - 40°23'31" Kuzey

YAĞIŞ ALANI : **78,50 km2** **YAKLAŞIK KOT : 1950 m**

GÖZLEM SÜRESİ : **13.04.1976 - 30.09.2006**

ORTALAMA AKIMLAR : **Gözlem süresinde 0.443 m3/sn. (26 Yıllık) 2006 Su yılında 0.364 m3/sn.**

ANLIK EN ÇOK VE EN AZ AKIMLAR:

2006 Su yılında anlık ençok akım	:	**3.34**	**m3/sn**	**01.04.2006**
2006 Su yılında anlık enaz akım	:	**0.001**	**m3/sn**	**06.12.2005**
Gözlem süresinde anlık ençok akım	:	**19.4**	**m3/sn**	**08.04.1991**
Gözlem süresinde anlık enaz akım	:	**0.000**	**m3/sn**	**13.12.2000**

Akımlar 01 Ekim 2005 'den 30 Eylül 2006' a kadar m3/sn olarak

Gün	Ekim	Kasım	Aralık	Ocak	Şubat	Mart	Nisan	Mayıs	Haziran	Temmuz	Ağustos	Eylül
01	0.120	0.320	0.120	0.055	0.055	0.055	2.71	2.01	0.520	1.37	0.243	0.298
02	0.120	0.220	0.120	0.055	0.055	0.055	1.92	1.64	0.520	0.502	0.203	0.298
03	0.120	0.120	0.120	0.055	0.055	0.055	2.29	1.04	0.520	1.02	0.203	0.243
04	0.120	0.120	0.170	0.055	0.055	0.055	1.36	1.73	0.520	0.700	0.203	0.243
05	0.120	0.120	0.120	0.055	0.055	0.055	0.880	1.04	0.465	0.502	0.298	0.243
06	0.120	0.170	0.055	0.055	0.055	0.055	1.11	1.19	0.465	0.370	0.298	0.203
07	0.170	0.270	0.055	0.055	0.055	0.055	0.958	1.73	0.465	0.320	0.243	0.203
08	0.120	0.220	0.055	0.055	0.055	0.055	0.958	1.11	0.465	0.320	0.243	0.203
09	0.120	0.170	0.055	0.055	0.055	0.055	1.27	1.04	0.465	0.320	0.243	0.203
10	0.120	0.120	0.055	0.055	0.055	0.055	1.27	0.958	0.465	0.320	0.243	0.243
11	0.120	0.120	0.055	0.055	0.055	0.055	1.27	0.880	0.465	0.270	0.243	0.243
12	0.120	0.120	0.055	0.055	0.055	0.055	1.11	0.880	0.409	0.270	0.243	0.243
13	0.120	0.120	0.055	0.055	0.055	0.055	1.11	0.880	0.409	0.270	0.298	0.243
14	0.120	0.120	0.055	0.055	0.055	0.055	1.04	0.880	0.354	0.220	0.354	0.243
15	0.120	0.120	0.055	0.055	0.055	0.055	1.04	0.880	0.354	0.220	0.298	0.298
16	0.120	0.120	0.055	0.055	0.055	0.055	1.19	0.880	0.354	0.220	0.298	0.298
17	0.120	0.120	0.055	0.055	0.055	0.055	1.11	0.808	0.354	0.220	0.298	0.298
18	0.120	0.120	0.055	0.055	0.055	0.220	1.04	0.808	0.354	0.220	0.298	0.298
19	0.120	0.120	0.055	0.055	0.055	0.370	0.958	0.736	0.354	0.170	0.298	0.298
20	0.120	0.120	0.055	0.055	0.055	0.370	0.958	0.736	0.354	0.170	0.298	0.298
21	0.120	0.120	0.055	0.055	0.055	0.436	1.27	0.736	0.298	0.170	0.298	0.298
22	0.120	0.120	0.055	0.055	0.055	0.436	1.27	0.736	0.298	0.170	0.298	0.298
23	0.120	0.220	0.055	0.055	0.055	0.370	1.36	0.736	0.243	0.170	0.298	0.298
24	0.120	0.170	0.055	0.055	0.055	0.436	1.82	0.592	0.243	0.170	0.354	0.298
25	0.120	0.120	0.055	0.055	0.055	0.780	1.45	0.592	0.243	0.170	0.298	0.298
26	0.120	0.120	0.055	0.055	0.055	1.19	1.19	0.592	0.243	0.170	0.243	0.298
27	0.120	0.120	0.055	0.055	0.055	1.10	0.958	0.520	0.243	0.243	0.243	0.298
28	0.120	0.120	0.055	0.055	0.055	1.65	0.958	0.520	0.243	0.243	0.243	0.298
29	0.120	0.120	0.055	0.055	-----	1.55	0.880	0.520	0.592	0.243	0.354	0.298
30	0.120	0.120	0.055	0.055	-----	1.65	1.27	0.520	0.664	0.243	0.354	0.298
31	0.270	-----	0.055	0.055	-----	2.38	-----	0.520	-----	0.243	0.298	-----
Maks.	0.270	0.502	0.220	0.055	0.055	2.92	3.34	2.75	1.04	1.95	0.664	0.409
Min.	0.120	0.078	0.001	0.055	0.055	0.055	0.592	0.520	0.243	0.170	0.203	0.203
Ortalama	0.126	0.147	0.067	0.055	0.055	0.448	1.27	0.917	0.398	0.330	0.278	0.271
LT/SN/Km2	1.61	1.87	0.855	0.701	0.701	5.70	16.1	11.7	5.07	4.20	3.55	3.45
AKIM mm.	4.31	4.84	2.29	1.88	1.69	15.3	41.8	31.3	13.1	11.3	9.50	8.94
MİL. M3	0.339	0.380	0.180	0.147	0.133	1.20	3.28	2.46	1.03	0.884	0.745	0.702

SU YILI (2006) YILLIK TOPLAM AKIM 11.48 MİLYON M3 146 MM. 4.6 LT/SN/Km2

24. Aras Havzasi

D24A049 DİGOR S. Hisarönü

YERİ : **KARS İLİ DIGOR ILÇESI HISARÖNÜ KÖYÜNÜN GIRIŞINDEDIR**
43°28'34" Doğu - 40°21'20" Kuzey

YAĞIŞ ALANI : **258,70 km2** **YAKLAŞIK KOT : 1585 m**

GÖZLEM SÜRESİ : **09.04.1976 - 30.09.2006**

ORTALAMA AKIMLAR : **Gözlem süresinde 0.902 m3/sn. (28 Yıllık) 2006 Su yılında 0.864 m3/sn.**

ANLIK EN ÇOK VE EN AZ AKIMLAR:

2006 Su yılında anlık ençok akım	**:**	**7.75**	**m3/sn**	**27.03.2006**
2006 Su yılında anlık enaz akım	**:**	**0.220**	**m3/sn**	**13.07.2006**
Gözlem süresinde anlık ençok akım	**:**	**31.4**	**m3/sn**	**13.04.1992**
Gözlem süresinde anlık enaz akım	**:**	**0.000**	**m3/sn**	**01.10.1979**

Akımlar 01 Ekim 2005 'den 30 Eylül 2006' a kadar m3/sn olarak

Gün	Ekim	Kasım	Aralık	Ocak	Şubat	Mart	Nisan	Mayıs	Haziran	Temmuz	Ağustos	Eylül
01	1.04	1.14	0.535	0.840	0.840	0.840	2.65	0.566	0.760	2.47	0.566	0.390
02	0.940	0.760	0.760	0.840	0.840	0.840	2.65	0.830	0.760	1.35	0.566	0.390
03	0.940	0.940	0.840	0.840	0.840	0.840	2.29	0.960	1.04	1.80	0.478	0.390
04	1.04	0.840	0.840	0.840	0.840	0.840	2.47	1.22	0.654	4.08	0.478	0.325
05	1.04	1.04	0.840	0.840	0.840	0.840	3.02	1.09	0.566	1.48	0.390	0.325
06	0.940	0.760	0.840	0.840	0.840	0.840	3.02	0.960	0.478	1.09	0.390	0.265
07	0.940	1.04	0.840	0.840	0.840	0.840	3.20	1.35	0.654	0.960	0.390	0.265
08	0.940	1.04	0.840	0.840	0.840	0.840	2.84	1.48	0.566	0.830	0.325	0.325
09	0.940	0.940	0.840	0.840	0.840	0.840	2.65	1.22	0.566	0.742	0.325	0.325
10	0.940	0.760	0.840	0.840	0.840	0.840	2.29	1.09	0.566	0.654	0.325	0.325
11	0.940	0.840	0.840	0.840	0.840	0.840	1.22	0.742	0.478	0.654	0.325	0.325
12	0.940	0.760	0.840	0.840	0.840	0.840	0.830	0.960	0.478	0.654	0.325	0.325
13	0.940	0.600	0.840	0.840	0.840	0.840	0.390	0.830	0.478	0.478	0.325	0.325
14	0.840	0.760	0.840	0.840	0.840	0.840	0.478	1.14	0.478	0.478	0.325	0.325
15	0.840	0.760	0.840	0.840	0.840	0.840	0.390	1.04	0.478	0.478	0.325	0.325
16	0.840	0.760	0.840	0.840	0.840	0.840	0.830	0.840	0.478	0.478	0.390	0.390
17	0.760	0.760	0.840	0.840	0.840	0.840	1.35	0.760	0.566	0.478	0.325	0.390
18	0.760	0.840	0.840	0.840	0.840	0.840	0.742	0.690	0.566	0.566	0.325	0.390
19	0.760	0.840	0.840	0.840	0.840	0.840	0.478	0.760	0.566	0.390	0.265	0.325
20	0.760	0.840	0.840	0.840	0.840	0.840	0.478	0.600	0.654	0.390	0.265	0.325
21	0.760	0.840	0.840	0.840	0.840	0.840	0.390	0.760	0.654	0.478	0.325	0.325
22	0.760	0.840	0.840	0.840	0.840	0.840	0.390	0.940	0.654	0.478	0.325	0.325
23	0.760	0.840	0.840	0.840	0.840	0.840	0.478	0.940	0.566	0.390	0.325	0.325
24	0.760	0.760	0.840	0.840	0.840	0.690	1.22	0.840	0.478	0.390	0.265	0.325
25	0.760	0.690	0.840	0.840	0.840	2.18	0.654	0.690	0.478	0.390	0.654	0.325
26	0.760	0.690	0.840	0.840	0.840	3.48	0.742	0.840	0.566	0.478	0.566	0.325
27	0.760	0.840	0.840	0.840	0.840	7.75	0.566	0.760	0.654	0.478	0.390	0.325
28	0.760	0.760	0.840	0.840	0.840	6.75	0.566	0.840	0.654	0.478	0.390	0.325
29	0.760	0.840	0.840	0.840	-----	5.50	0.478	0.840	1.09	0.566	0.390	0.325
30	0.690	0.940	0.840	0.840	-----	4.08	0.390	0.840	1.80	0.478	0.390	0.325
31	0.940	-----	0.840	0.840	-----	3.20	-----	0.940	-----	0.566	0.478	-----
Maks.	1.48	1.48	1.04	0.840	0.840	7.75	5.26	2.47	2.47	5.26	0.830	0.390
Min.	0.600	0.600	0.465	0.840	0.840	0.535	0.390	0.465	0.465	0.220	0.220	0.265
Ortalama	0.856	0.835	0.828	0.840	0.840	1.71	1.34	0.915	0.647	0.828	0.385	0.334
LT/SN/Km2	3.31	3.23	3.20	3.25	3.25	6.60	5.17	3.54	2.50	3.20	1.49	1.29
AKIM mm.	8.87	8.37	8.57	8.70	7.86	17.7	13.4	9.47	6.49	8.57	3.98	3.35
MİL. M3	2.29	2.17	2.22	2.25	2.03	4.57	3.47	2.45	1.68	2.22	1.03	0.866

SU YILI (2006) YILLIK TOPLAM AKIM 27.25 MİLYON M3 105 MM. 3.3 LT/SN/Km2

24. Aras Havzasi

D24A050 KAYINLIK D. BALÇEŞME

YERİ : **KARS GÖLE YOLUNDA BALÇEŞME KÖYÜNDEDİR.**
42°49'1" Doğu - 40°50'17" Kuzey

YAĞIŞ ALANI : **195,00 km2** **YAKLAŞIK KOT : 2200 m**

GÖZLEM SÜRESİ : **01.10.1976 - 30.09.2006**

ORTALAMA AKIMLAR : **Gözlem süresinde 3.096 m3/sn. (2 Yıllık) 2006 Su yılında 3.096 m3/sn.**

ANLIK EN ÇOK VE EN AZ AKIMLAR:

2006 Su yılında anlık ençok akım	**:**	**27.8**	**m3/sn**	**28.04.2006**
2006 Su yılında anlık enaz akım	**:**	**0.371**	**m3/sn**	**13.10.2005**
Gözlem süresinde anlık ençok akım	**:**	**65.4**	**m3/sn**	**07.04.2000**
Gözlem süresinde anlık enaz akım	**:**	**0.300**	**m3/sn**	**26.10.1999**

Akımlar 01 Ekim 2005 'den 30 Eylül 2006' a kadar m3/sn olarak

Gün	Ekim	Kasım	Aralık	Ocak	Şubat	Mart	Nisan	Mayıs	Haziran	Temmuz	Ağustos	Eylül
01	0.585	6.10	0.728	0.728	0.728	0.728	3.87	12.0	3.66	1.60	2.82	2.40
02	0.514	4.29	0.728	0.728	0.728	0.728	5.14	20.2	3.45	2.08	3.24	1.60
03	0.514	4.08	0.728	0.728	0.728	0.728	6.74	12.8	5.78	2.08	3.03	1.12
04	0.585	3.24	0.728	0.728	0.728	0.728	13.2	12.4	6.74	2.40	3.03	0.657
05	0.514	2.40	0.728	0.728	0.728	0.728	16.3	9.45	6.74	1.76	2.82	0.585
06	0.442	2.82	0.728	0.728	0.728	0.728	9.80	9.80	6.10	1.60	2.82	0.585
07	0.442	2.82	0.728	0.728	0.728	0.728	8.05	11.2	2.82	1.44	2.61	0.585
08	0.442	2.82	0.728	0.728	0.728	0.728	7.70	10.5	2.61	3.66	2.61	0.585
09	0.442	2.40	0.728	0.728	0.728	0.728	8.40	15.2	2.40	3.66	2.61	0.514
10	0.407	2.24	0.728	0.728	0.728	0.728	11.6	17.4	2.24	3.66	2.61	0.514
11	0.407	1.76	0.728	0.728	0.728	0.728	14.8	14.8	2.08	3.66	2.61	0.585
12	0.407	1.28	0.728	0.728	0.728	0.728	15.8	13.6	2.08	3.24	2.61	0.585
13	0.407	1.12	0.728	0.728	0.728	0.728	12.0	13.2	1.92	3.03	2.61	0.585
14	0.407	1.12	0.728	0.728	0.728	0.728	13.2	12.8	1.92	3.24	2.40	0.657
15	0.407	1.12	0.728	0.728	0.728	0.728	13.6	11.2	1.76	3.24	2.40	0.657
16	0.407	0.800	0.728	0.728	0.728	0.728	16.9	9.80	1.60	3.03	2.40	0.585
17	1.92	0.800	0.728	0.728	0.728	0.728	13.2	10.2	1.60	3.24	2.40	0.585
18	1.12	0.800	0.728	0.728	0.728	0.728	12.4	9.80	1.60	3.03	2.40	0.514
19	0.728	0.800	0.728	0.728	0.728	0.728	9.80	8.75	1.44	3.03	2.82	0.514
20	1.12	0.728	0.728	0.728	0.728	0.728	8.75	8.05	1.60	3.03	3.03	0.514
21	0.960	0.728	0.728	0.728	0.728	0.728	11.6	8.75	1.60	3.03	2.82	0.514
22	0.960	0.728	0.728	0.728	0.728	0.728	11.6	7.38	1.44	2.82	2.82	0.514
23	0.800	0.728	0.728	0.728	0.728	0.728	10.5	6.74	1.60	2.82	3.03	0.514
24	0.728	0.728	0.728	0.728	0.728	0.728	13.6	6.10	1.76	2.82	3.03	0.585
25	0.728	0.728	0.728	0.728	0.728	0.728	14.4	5.46	1.44	2.82	2.82	0.585
26	0.728	0.728	0.728	0.728	0.728	0.728	19.7	5.14	1.28	2.82	2.82	0.585
27	0.728	0.728	0.728	0.728	0.728	0.728	23.6	5.14	1.44	2.82	2.82	0.514
28	0.800	0.728	0.728	0.728	0.728	0.442	27.8	5.14	1.28	2.82	2.61	0.585
29	0.960	0.728	0.728	0.728	-----	4.08	20.2	4.50	1.28	2.82	2.61	0.514
30	0.728	0.728	0.728	0.728	-----	3.87	12.8	4.08	1.44	2.82	2.61	0.514
31	2.82	-----	0.728	0.728	-----	3.87	-----	3.66	-----	2.82	2.61	-----
Maks.	4.08	8.05	0.728	0.728	0.728	5.78	27.8	24.3	9.45	5.78	4.29	3.66
Min.	0.371	0.728	0.728	0.728	0.728	0.442	1.12	3.66	1.12	1.28	1.76	0.371
Ortalama	0.747	1.69	0.728	0.728	0.728	1.03	12.9	9.85	2.49	2.80	2.73	0.678
LT/SN/Km2	3.83	8.69	3.73	3.73	3.73	5.28	66.2	50.5	12.8	14.4	14.0	3.48
AKIM mm.	10.3	22.5	10.00	10.00	9.03	14.1	171.	135.	33.1	38.5	37.4	9.02
MİL. M3	2.00	4.39	1.95	1.95	1.76	2.76	33.4	26.4	6.45	7.51	7.30	1.76

SU YILI (2006) YILLIK TOPLAM AKIM 97.63 MİLYON M3 501 MM. 15.9 LT/SN/Km2

24. Aras Havzasi

D24A053 KURA N. ÇATALKÖPRÜ

YERİ : **ARDAHAN-BÜLBÜLHAN YOLUNUN TAKRİBEN 22.KM.SINDEKI KURA NEHRININ KESTIĞI ÇATAL KÖPRÜ KÖYÜNDEDIR.**
42°29'9" Doğu - 40°4'20" Kuzey

YAĞIŞ ALANI : **1613,20 km2** **YAKLAŞIK KOT : 1850 m**

GÖZLEM SÜRESİ : **12.11.1976 - 30.09.2006**

ORTALAMA AKIMLAR : **Gözlem süresinde 11.476 m3/sn. (28 Yıllık) 2006 Su yılında 16.934 m3/sn.**

ANLIK EN ÇOK VE EN AZ AKIMLAR:

2006 Su yılında anlık ençok akım	:	**142.**	**m3/sn**	**03.05.2006**
2006 Su yılında anlık enaz akım	:	**2.62**	**m3/sn**	**24.11.2005**
Gözlem süresinde anlık ençok akım	:	**335.**	**m3/sn**	**02.05.1987**
Gözlem süresinde anlık enaz akım	:	**0.940**	**m3/sn**	**05.10.1986**

Akımlar 01 Ekim 2005 'den 30 Eylül 2006' a kadar m3/sn olarak

Gün	Ekim	Kasım	Aralık	Ocak	Şubat	Mart	Nisan	Mayıs	Haziran	Temmuz	Ağustos	Eylül
01	5.77	5.50	5.02	5.02	5.02	5.50	76.2	73.1	14.2	5.50	3.90	3.13
02	5.26	5.50	5.02	5.02	5.02	5.50	102.	92.9	13.4	6.04	3.90	3.13
03	5.02	5.50	5.02	5.02	5.02	5.50	106.	131.	13.0	6.85	3.90	2.95
04	4.78	5.50	5.02	5.02	5.02	5.50	104.	119.	14.2	7.81	4.10	2.95
05	5.02	5.50	5.02	5.02	5.02	5.50	94.0	101.	14.2	9.85	3.70	2.95
06	5.02	5.50	5.02	5.02	5.02	5.50	78.3	88.3	12.6	9.15	3.70	2.95
07	4.78	5.50	5.02	5.02	5.02	5.50	64.0	84.8	12.2	7.17	3.50	2.95
08	4.78	5.50	5.02	5.02	5.02	6.04	52.7	83.7	11.0	7.81	3.50	2.95
09	4.78	5.50	5.02	5.02	5.02	6.04	60.5	86.0	9.85	6.85	3.50	2.95
10	4.54	5.50	5.02	5.02	5.02	6.04	76.2	88.3	9.15	6.31	3.50	2.95
11	4.54	5.50	5.02	5.02	5.02	6.04	90.6	82.5	8.45	6.31	3.50	2.95
12	4.54	5.50	5.02	5.02	5.02	6.04	92.9	74.1	7.49	6.04	3.50	2.95
13	4.54	5.50	5.02	5.02	5.02	6.04	94.0	67.6	7.49	5.02	3.32	2.95
14	4.30	5.50	5.02	5.02	5.02	6.04	89.4	62.2	6.85	4.78	3.32	2.95
15	4.54	5.50	5.02	5.02	5.02	6.04	84.8	56.9	6.31	4.54	3.13	2.95
16	4.54	5.50	5.02	5.02	5.02	6.04	88.3	52.7	5.77	4.54	3.13	2.95
17	6.31	5.50	5.02	5.02	5.02	5.77	92.9	51.2	5.02	4.78	3.13	2.95
18	9.15	5.50	5.02	5.02	5.02	6.31	87.1	49.6	5.02	4.54	3.13	3.13
19	8.80	5.26	5.02	5.02	5.02	6.85	76.2	42.9	4.78	4.54	3.32	2.95
20	8.13	5.26	5.02	5.02	5.02	7.49	66.7	38.6	4.78	4.54	3.50	2.95
21	8.45	5.02	5.02	5.02	5.02	8.80	65.8	45.8	5.26	4.54	3.90	2.95
22	8.45	4.78	5.02	5.02	5.02	9.15	72.0	43.6	5.02	4.10	4.54	2.95
23	8.13	5.02	5.02	5.02	5.02	9.50	90.6	36.5	4.78	4.10	3.90	2.95
24	7.49	5.02	5.02	5.02	5.02	10.6	106.	30.9	4.78	3.90	3.50	2.95
25	6.58	5.02	5.02	5.02	5.02	11.0	113.	27.5	4.78	3.70	3.70	2.95
26	5.77	5.02	5.02	5.02	5.02	20.7	114.	24.9	4.78	3.70	3.70	3.13
27	5.50	5.02	5.02	5.02	5.02	33.6	94.0	22.5	4.78	3.70	3.50	3.13
28	5.50	5.02	5.02	5.02	5.02	37.9	79.4	21.9	5.02	3.50	3.50	3.13
29	5.50	5.02	5.02	5.02	-----	41.5	70.2	20.1	5.02	3.50	3.32	2.95
30	5.50	5.02	5.02	5.02	-----	46.5	68.4	17.4	5.26	3.70	3.13	3.13
31	5.50	-----	5.02	5.02	-----	56.1	-----	15.8	-----	3.70	3.13	-----
Maks.	9.85	5.50	5.02	5.02	5.02	61.3	127.	142.	17.4	11.4	5.02	3.70
Min.	4.30	2.62	5.02	5.02	5.02	5.50	49.6	14.7	4.78	3.50	3.13	2.95
Ortalama	5.86	5.32	5.02	5.02	5.02	13.1	85.0	59.1	7.84	5.33	3.55	2.99
LT/SN/Km2	3.63	3.30	3.11	3.11	3.11	8.09	52.7	36.7	4.86	3.30	2.20	1.85
AKIM mm.	9.72	8.54	8.33	8.33	7.53	21.7	137.	98.2	12.6	8.84	5.89	4.81
MİL. M3	15.7	13.8	13.4	13.4	12.1	35.0	220.	158.	20.3	14.3	9.50	7.76

SU YILI (2006) YILLIK TOPLAM AKIM 533.26 MİLYON M3 331 MM. 10.5 LT/SN/Km2

24. Aras Havzasi

D24A058 KIŞLA D. ÇAYIRDÜZÜ

YERİ : **HORASAN DAN SOLA AYRILAN ÇAYIRDÜZÜ KÖY YOLUNUN 20 KM İLERİSİNDEDİR.**
42°3'27" Doğu - 40°8'51" Kuzey

YAĞIŞ ALANI : **77,10 km2** **YAKLAŞIK KOT : 1760 m**

GÖZLEM SÜRESİ : **01.10.1979 - 30.09.2006**

ORTALAMA AKIMLAR : **Gözlem süresinde 0.555 m3/sn. (27 Yıllık) 2006 Su yılında 0.496 m3/sn.**

ANLIK EN ÇOK VE EN AZ AKIMLAR:

2006 Su yılında anlık ençok akım	**:**	**3.97**	**m3/sn**	**21.08.2006**
2006 Su yılında anlık enaz akım	**:**	**0.012**	**m3/sn**	**09.01.2006**
Gözlem süresinde anlık ençok akım	**:**	**49.9**	**m3/sn**	**06.07.1995**
Gözlem süresinde anlık enaz akım	**:**	**0.000**	**m3/sn**	**01.10.1991**

17. Anahtar Eğrisi (Seviyeler cm olarak)

Seviye	Akım	Seviye	Akım	Seviye	Akım	Seviye	Akım
1	0.000	11	0.212	25	1.5	90	12.2
3	0.005	13	0.330	35	2.9	110	15.8
5	0.021	15	0.480	45	4.4	120	17.6
7	0.058	17	0.650	55	6.0	130	19.4
9	0.120	19	0.835	70	8.6	140	21.2

Akımlar 01 Ekim 2005 'den 30 Eylül 2006' a kadar m3/sn olarak

Gün	Ekim	Kasım	Aralık	Ocak	Şubat	Mart	Nisan	Mayıs	Haziran	Temmuz	Ağustos	Eylül
01	0.160	0.480	0.212	0.085	0.021	0.212	0.835	2.60	0.650	0.400	0.120	0.058
02	0.160	0.400	0.212	0.085	0.021	0.212	1.05	2.45	0.730	0.560	0.120	0.058
03	0.160	0.330	0.212	0.085	0.021	0.212	1.28	2.30	0.835	0.400	0.160	0.058
04	0.212	0.270	0.212	0.085	0.036	0.212	1.51	2.60	0.730	0.560	0.160	0.058
05	0.212	0.270	0.212	0.085	0.036	0.212	1.51	2.45	0.650	0.560	0.160	0.058
06	0.212	0.270	0.212	0.085	0.036	0.270	1.51	2.45	0.650	0.480	0.160	0.058
07	0.212	0.270	0.212	0.036	0.058	0.270	1.51	2.75	0.560	0.400	0.160	0.058
08	0.212	0.270	0.212	0.021	0.085	0.270	1.89	2.90	0.480	0.400	0.160	0.058
09	0.212	0.270	0.212	0.012	0.160	0.270	2.45	2.75	0.480	0.330	0.160	0.058
10	0.212	0.270	0.212	0.021	0.160	0.270	2.60	2.75	0.400	0.330	0.160	0.058
11	0.212	0.270	0.212	0.021	0.160	0.270	2.30	2.45	0.330	0.270	0.160	0.058
12	0.212	0.212	0.212	0.021	0.160	0.270	2.60	2.45	0.330	0.270	0.160	0.058
13	0.212	0.212	0.160	0.021	0.160	0.270	2.60	2.30	0.330	0.212	0.160	0.058
14	0.160	0.212	0.160	0.021	0.160	0.270	2.75	2.15	0.330	0.212	0.085	0.058
15	0.160	0.212	0.160	0.021	0.160	0.270	2.75	2.15	0.270	0.212	0.085	0.036
16	0.160	0.212	0.212	0.021	0.120	0.270	3.05	2.15	0.270	0.160	0.120	0.058
17	0.650	0.212	0.212	0.021	0.160	0.270	2.90	1.77	0.270	0.160	0.120	0.058
18	0.270	0.160	0.212	0.021	0.120	0.270	2.75	1.39	0.270	0.160	0.120	0.058
19	0.270	0.160	0.212	0.036	0.120	0.270	2.45	1.39	0.270	0.212	0.120	0.058
20	0.270	0.212	0.212	0.036	0.120	0.270	2.30	1.39	0.212	0.212	0.120	0.085
21	0.212	0.212	0.212	0.021	0.120	0.212	2.75	1.28	0.270	0.212	0.212	0.085
22	0.212	0.212	0.160	0.021	0.120	0.270	2.15	1.28	0.270	0.160	0.160	0.085
23	0.212	0.160	0.160	0.021	0.120	0.270	2.15	1.16	0.212	0.120	0.120	0.085
24	0.160	0.160	0.212	0.021	0.120	0.330	2.15	1.16	0.212	0.085	0.120	0.085
25	0.160	0.160	0.160	0.021	0.120	0.400	2.30	1.05	0.212	0.085	0.120	0.085
26	0.160	0.212	0.120	0.021	0.058	0.400	2.15	0.930	0.212	0.120	0.120	0.085
27	0.160	0.212	0.085	0.021	0.021	0.400	2.30	0.835	0.212	0.085	0.085	0.085
28	0.160	0.212	0.085	0.021	0.160	0.480	2.45	0.835	0.212	0.085	0.058	0.085
29	0.270	0.212	0.085	0.021	-----	0.480	2.30	0.835	0.212	0.120	0.085	0.085
30	0.212	0.212	0.085	0.021	-----	0.560	2.75	0.835	0.270	0.120	0.085	0.085
31	0.480	-----	0.085	0.021	-----	0.650	-----	0.730	-----	0.120	0.058	-----
Maks.	1.28	0.560	0.270	0.085	0.212	0.650	3.05	3.50	1.28	3.05	3.97	0.085
Min.	0.160	0.120	0.058	0.012	0.012	0.160	0.835	0.650	0.212	0.085	0.058	0.036
Ortalama	0.224	0.238	0.178	0.035	0.104	0.308	2.20	1.82	0.378	0.252	0.129	0.067
LT/SN/Km2	2.90	3.09	2.31	0.448	1.35	4.00	28.6	23.6	4.90	3.27	1.67	0.871
AKIM mm.	7.77	8.00	6.20	1.20	3.26	10.7	74.0	63.3	12.7	8.75	4.47	2.26
MİL. M3	0.599	0.617	0.478	0.093	0.252	0.826	5.71	4.88	0.980	0.675	0.345	0.174

SU YILI (2006) YILLIK TOPLAM AKIM 15.63 MİLYON M3 203 MM. 6.4 LT/SN/Km2

24. Aras Havzasi

D24A060 KÖYALTI D. ÇATALÖREN

YERİ : **ERZURUM HINIS YOLU 61. KM SİNDEKİ YAĞAN KÖYÜNDE YSE YOLU ÜZERİNDEKİ ÇATALÖREN KÖYÜNDEDİR**

42°1'38" Doğu - 39°47'18" Kuzey

YAĞIŞ ALANI : **73,40 km2** **YAKLAŞIK KOT : 2225 m**

GÖZLEM SÜRESİ : **01.10.1982 - 30.09.2006**

ORTALAMA AKIMLAR : **Gözlem süresinde 0.828 m3/sn. (24 Yıllık) 2006 Su yılında 0.988 m3/sn.**

ANLIK EN ÇOK VE EN AZ AKIMLAR:

2006 Su yılında anlık ençok akım	**:**	**18.4**	**m3/sn**	**16.04.2006**
2006 Su yılında anlık enaz akım	**:**	**0.001**	**m3/sn**	**30.03.2006**
Gözlem süresinde anlık ençok akım	**:**	**35.0**	**m3/sn**	**25.04.2005**
Gözlem süresinde anlık enaz akım	**:**	**0.001**	**m3/sn**	**30.03.2006**

10. Anahtar Eğrisi (Seviyeler cm olarak)

Seviye	Akım	Seviye	Akım	Seviye	Akım	Seviye	Akım
40	0.130	50	0.684	60	1.5	160	17.6
42	0.210	52	0.819	80	3.7	170	19.5
44	0.320	54	0.970	100	6.4	180	21.6
46	0.438	56	1.1	120	10.0	190	23.8
48	0.556	58	1.3	140	13.8	200	26.0

Akımlar 01 Ekim 2005 'den 30 Eylül 2006' a kadar m3/sn olarak

Gün	Ekim	Kasım	Aralık	Ocak	Şubat	Mart	Nisan	Mayıs	Haziran	Temmuz	Ağustos	Eylül
01	0.185	0.330	0.243	0.185	0.185	0.185	0.185	4.74	0.414	0.243	0.372	0.330
02	0.167	0.301	0.243	0.185	0.185	0.185	0.800	4.22	0.372	0.272	0.372	0.330
03	0.185	0.272	0.214	0.185	0.185	0.185	1.34	4.48	0.372	0.498	0.330	0.301
04	0.185	0.243	0.243	0.185	0.185	0.185	1.57	6.95	0.372	0.414	0.330	0.301
05	0.185	0.243	0.243	0.185	0.185	0.185	2.22	3.83	0.330	0.372	0.330	0.301
06	0.167	0.243	0.243	0.185	0.185	0.185	1.85	6.62	0.330	0.330	0.301	0.301
07	0.167	0.243	0.214	0.185	0.185	0.185	1.85	5.87	0.330	0.272	0.272	0.301
08	0.185	0.243	0.214	0.185	0.185	0.185	1.85	6.16	0.272	0.243	0.330	0.301
09	0.214	0.243	0.243	0.185	0.185	0.185	3.31	4.61	0.272	0.243	0.330	0.301
10	0.214	0.214	0.272	0.185	0.185	0.185	5.58	3.83	0.243	0.243	0.330	0.301
11	0.185	0.214	0.301	0.185	0.185	0.185	7.77	2.31	0.243	0.243	0.372	0.301
12	0.185	0.214	0.301	0.185	0.185	0.185	10.0	2.03	0.214	0.243	0.414	0.301
13	0.185	0.214	0.372	0.185	0.185	0.185	11.0	1.85	0.214	0.243	0.330	0.301
14	0.167	0.214	0.330	0.185	0.185	0.185	11.9	1.76	0.243	0.243	0.372	0.301
15	0.185	0.214	0.301	0.185	0.185	0.185	13.2	1.57	0.214	0.243	0.330	0.301
16	0.243	0.214	0.272	0.185	0.185	0.185	14.8	1.26	0.185	0.243	0.330	0.330
17	0.748	0.185	0.272	0.185	0.185	0.185	12.7	1.19	0.185	0.243	0.330	0.330
18	0.540	0.185	0.272	0.185	0.185	0.185	13.0	1.12	0.185	0.243	0.330	0.330
19	0.330	0.214	0.272	0.185	0.185	0.185	8.86	1.06	0.185	0.243	0.414	0.330
20	0.301	0.214	0.301	0.185	0.185	0.185	8.29	1.06	0.185	0.243	0.414	0.330
21	0.243	0.214	0.330	0.185	0.185	0.185	11.9	1.41	0.243	0.243	0.330	0.372
22	0.214	0.214	0.301	0.185	0.185	0.185	9.24	1.06	0.185	0.243	0.372	0.372
23	0.185	0.214	0.301	0.185	0.185	0.185	7.94	0.928	0.185	0.243	0.330	0.372
24	0.185	0.243	0.330	0.185	0.185	0.185	12.7	0.800	0.185	0.243	0.330	0.372
25	0.185	0.243	0.372	0.185	0.185	0.185	11.1	0.748	0.185	0.272	0.330	0.372
26	0.185	0.301	0.372	0.185	0.185	0.167	6.16	0.644	0.185	0.272	0.330	0.372
27	0.243	0.272	0.330	0.185	0.185	0.082	4.87	0.592	0.185	0.272	0.330	0.372
28	0.330	0.272	0.301	0.185	0.185	0.096	3.05	0.540	0.243	0.272	0.330	0.372
29	0.498	0.272	0.330	0.185	-----	0.167	2.66	0.540	0.243	0.330	0.330	0.372
30	0.696	0.243	0.330	0.185	-----	0.167	6.78	0.498	0.214	0.330	0.330	0.372
31	0.592	-----	0.301	0.185	-----	0.132	-----	0.456	-----	0.330	0.330	-----
Maks.	0.928	0.330	0.414	0.185	0.185	0.185	18.4	11.1	0.456	1.76	0.414	0.372
Min.	0.149	0.167	0.214	0.185	0.185	0.001	0.050	0.414	0.167	0.214	0.272	0.272
Ortalama	0.274	0.238	0.289	0.185	0.185	0.175	6.95	2.41	0.247	0.278	0.342	0.331
LT/SN/Km2	3.73	3.24	3.94	2.52	2.52	2.39	94.7	32.8	3.37	3.78	4.66	4.52
AKIM mm.	9.98	8.41	10.6	6.75	6.10	6.40	245.	88.0	8.73	10.1	12.5	11.7
MİL. M3	0.733	0.617	0.774	0.496	0.448	0.470	18.0	6.46	0.640	0.744	0.916	0.859

SU YILI (2006) YILLIK TOPLAM AKIM 31.16 MİLYON M3 424 MM. 13.5 LT/SN/Km2

24. Aras Havzasi

D24A063 COT S. KOYUNPİNARI

YERİ : **ARDAHAN İLİ HANAK İLÇESINE 10 KM MESAFEDE KOYUNPINAR KÖYÜNDEDİR.**
42°46'37" Doğu - 41°14'24" Kuzey

YAĞIŞ ALANI : **240,22 km2** **YAKLAŞIK KOT : 1839 m**

GÖZLEM SÜRESİ : **01.10.1984 - 30.09.2006**

ORTALAMA AKIMLAR : **Gözlem süresinde 3.163 m3/sn. (19 Yıllık) 2006 Su yılında 1.901 m3/sn.**

ANLIK EN ÇOK VE EN AZ AKIMLAR:

2006 Su yılında anlık ençok akım	**:**	**14.1**	**m3/sn**	**03.05.2006**
2006 Su yılında anlık enaz akım	**:**	**0.180**	**m3/sn**	**08.06.2006**
Gözlem süresinde anlık ençok akım	**:**	**43.0**	**m3/sn**	**21.05.1987**
Gözlem süresinde anlık enaz akım	**:**	**0.082**	**m3/sn**	**14.11.1984**

Akımlar 01 Ekim 2005 'den 30 Eylül 2006' a kadar m3/sn olarak

Gün	Ekim	Kasım	Aralık	Ocak	Şubat	Mart	Nisan	Mayıs	Haziran	Temmuz	Ağustos	Eylül
01	0.830	0.830	0.830	0.830	0.830	1.37	1.37	11.5	5.90	2.07	0.298	0.725
02	1.52	0.830	0.830	0.830	0.830	1.37	1.37	11.8	5.90	2.07	0.370	0.625
03	1.10	0.965	0.830	0.830	0.830	1.37	1.88	14.1	5.62	1.96	0.370	0.625
04	0.965	0.830	0.830	0.830	0.830	1.37	1.88	12.1	5.62	1.07	0.370	0.625
05	0.830	0.830	0.830	0.830	0.830	1.88	2.43	11.8	5.40	1.07	0.298	0.625
06	0.725	0.965	0.830	0.830	0.830	1.70	2.63	11.8	5.18	1.48	0.298	0.625
07	0.725	0.830	0.830	0.830	0.830	2.07	3.03	9.80	4.96	1.07	0.298	0.725
08	0.725	0.625	0.830	0.830	0.830	2.43	2.43	8.40	5.18	1.48	0.298	0.725
09	0.725	0.725	0.830	0.830	0.830	3.23	3.23	8.68	3.87	0.948	0.298	0.725
10	0.725	1.10	0.830	0.830	0.830	1.88	3.87	8.96	3.23	1.20	0.233	0.625
11	0.725	1.10	0.830	0.830	0.830	1.88	3.03	8.96	3.03	1.96	0.233	0.625
12	0.725	0.965	0.830	0.830	0.830	1.88	2.25	8.12	2.63	1.32	0.233	0.625
13	0.830	0.965	0.830	0.830	0.830	1.88	2.63	7.84	2.43	0.700	0.233	0.625
14	0.830	0.830	0.830	0.830	0.830	1.88	3.03	7.56	2.43	0.610	0.233	0.625
15	0.965	0.830	0.830	0.830	0.830	2.83	3.03	7.00	2.25	0.610	0.233	0.625
16	1.21	0.965	0.830	0.830	0.830	5.90	2.25	6.72	1.88	0.610	0.182	0.725
17	1.10	0.830	0.830	0.830	0.830	5.18	2.83	6.17	1.70	0.530	0.182	0.725
18	0.965	0.355	0.830	0.830	0.830	1.70	2.83	5.90	1.70	0.530	0.233	0.725
19	0.965	0.435	0.830	0.830	0.830	1.37	2.43	5.40	1.70	0.530	0.370	0.625
20	0.965	0.520	0.830	0.830	0.830	1.37	2.63	4.08	1.70	0.530	0.370	0.625
21	0.830	0.520	0.830	0.830	0.830	1.37	2.63	4.30	1.52	0.530	0.440	0.625
22	0.965	0.520	0.830	0.830	0.830	1.37	3.03	5.18	1.88	0.530	1.10	0.625
23	0.830	0.520	0.830	0.830	0.830	1.37	3.23	7.00	1.70	0.440	0.830	0.725
24	0.830	0.520	0.830	0.830	0.830	1.37	2.83	6.17	1.70	0.370	0.830	0.830
25	0.830	0.520	0.830	0.830	0.830	1.10	3.03	7.84	1.52	0.370	0.725	0.830
26	0.830	0.625	0.830	0.830	0.830	0.830	3.65	8.96	1.52	0.370	0.830	0.725
27	0.830	0.520	0.830	0.830	0.830	1.21	7.00	7.84	1.52	0.440	0.830	0.725
28	0.830	0.520	0.830	0.830	0.830	1.21	8.96	7.56	1.88	0.370	0.725	0.725
29	0.830	0.830	0.830	0.830	-----	1.10	12.1	7.28	2.25	0.370	0.725	0.725
30	0.965	0.830	0.830	0.830	-----	0.830	11.8	6.17	2.63	0.370	0.725	0.725
31	0.830	-----	0.830	0.830	-----	0.965	-----	5.90	-----	0.370	0.725	-----
Maks.	2.25	1.10	0.830	0.830	0.830	7.56	12.1	14.1	5.90	3.02	1.10	0.965
Min.	0.520	0.290	0.830	0.830	0.830	0.625	1.37	4.08	0.180	0.370	0.182	0.625
Ortalama	0.889	0.742	0.830	0.830	0.830	1.85	3.64	8.09	3.01	0.867	0.455	0.682
LT/SN/Km2	3.70	3.09	3.46	3.46	3.46	7.69	15.2	33.7	12.5	3.61	1.90	2.84
AKIM mm.	9.91	8.00	9.25	9.25	8.36	20.6	39.3	90.2	32.5	9.67	5.08	7.36
MİL. M3	2.38	1.92	2.22	2.22	2.01	4.95	9.45	21.7	7.81	2.32	1.22	1.77

SU YILI (2006) YILLIK TOPLAM AKIM 59.97 MİLYON M3 250 MM. 7.9 LT/SN/Km2

24. Aras Havzasi

D24A066 ARAS N. HALİMCAN KARAKOL.

YERİ : **TUZLUCA - HALIKIŞLAK YOLU ÜZERİNDEKI ERGÜDER KÖPRÜSÜNÜN 500 M. KADAR MANSABINDADIR**

43°38'13" Doğu - 40°7'54" Kuzey

YAĞIŞ ALANI : **10272,00 km2** **YAKLAŞIK KOT : 970 m**

GÖZLEM SÜRESİ : **01.10.1984 - 30.09.2006**

ORTALAMA AKIMLAR : **Gözlem süresinde 56.525 m3/sn. (11 Yıllık) 2006 Su yılında 69.291 m3/sn.**

ANLIK EN ÇOK VE EN AZ AKIMLAR:

2006 Su yılında anlık ençok akım	**:**	**466.**	**m3/sn**	**01.04.2006**
2006 Su yılında anlık enaz akım	**:**	**12.0**	**m3/sn**	**19.08.2006**
Gözlem süresinde anlık ençok akım	**:**	**836.**	**m3/sn**	**28.04.1997**
Gözlem süresinde anlık enaz akım	**:**	**1.00**	**m3/sn**	**29.12.1987**

Akımlar 01 Ekim 2005 'den 30 Eylül 2006' a kadar m3/sn olarak

Gün	Ekim	Kasım	Aralık	Ocak	Şubat	Mart	Nisan	Mayıs	Haziran	Temmuz	Ağustos	Eylül
01	17.2	25.2	28.0	30.9	19.4	28.0	466.	255.	72.0	30.5	18.3	13.6
02	18.3	25.9	27.3	30.9	19.4	28.8	450.	264.	63.6	32.8	17.8	13.6
03	18.9	28.0	30.2	30.2	19.4	29.5	420.	316.	62.4	40.8	17.8	13.2
04	20.6	30.2	28.8	30.2	19.4	30.2	410.	348.	61.2	47.1	17.8	13.2
05	22.6	31.6	27.3	30.2	19.4	29.5	380.	384.	61.2	48.0	17.3	13.2
06	20.0	28.8	25.9	25.9	19.4	29.5	362.	422.	62.4	45.3	16.8	12.8
07	23.2	30.9	25.2	19.4	19.4	29.5	352.	440.	60.0	39.9	15.8	12.8
08	21.3	30.2	25.2	19.4	19.4	29.5	340.	402.	60.0	35.9	15.8	13.2
09	21.9	28.0	25.2	19.4	19.4	35.4	318.	382.	58.8	32.8	15.8	13.2
10	21.3	25.9	25.9	19.4	19.4	54.0	296.	350.	52.8	30.5	14.9	13.2
11	21.3	27.3	28.0	19.4	19.4	52.8	271.	320.	50.4	28.5	14.5	13.2
12	18.3	26.6	27.3	19.4	19.4	46.8	229.	318.	48.0	26.5	14.5	13.2
13	17.8	29.5	28.8	19.4	19.4	44.4	212.	316.	44.4	25.8	14.0	13.2
14	18.9	30.9	30.2	19.4	19.4	43.2	224.	360.	42.0	25.8	13.6	13.2
15	20.0	31.6	29.5	19.4	19.4	43.2	229.	280.	40.4	25.2	13.2	13.2
16	20.6	28.8	28.8	19.4	19.4	44.4	219.	229.	38.7	25.2	13.2	13.6
17	20.6	30.2	29.5	19.4	19.4	44.4	244.	203.	37.1	25.2	13.2	14.0
18	20.6	32.4	26.6	19.4	19.4	44.4	257.	149.	36.3	25.2	12.4	14.5
19	21.9	30.9	27.3	19.4	19.4	67.2	237.	127.	35.4	25.2	12.0	14.5
20	24.6	27.3	27.3	19.4	19.4	142.	264.	127.	27.9	18.8	12.8	14.5
21	23.2	25.9	26.6	19.4	19.4	156.	280.	117.	25.2	17.8	13.2	14.9
22	22.6	25.9	25.9	19.4	20.0	149.	310.	96.0	24.5	17.3	14.5	15.4
23	19.4	26.6	25.9	19.4	20.0	144.	322.	93.0	23.9	16.8	15.8	15.4
24	18.9	25.2	24.6	19.4	20.0	173.	350.	82.5	23.4	16.8	15.8	15.4
25	18.3	25.2	25.2	19.4	20.0	186.	300.	78.0	23.4	15.8	14.9	15.8
26	19.4	24.6	25.2	19.4	20.6	191.	276.	67.2	23.9	15.8	14.5	15.8
27	20.6	25.9	25.9	19.4	22.6	186.	262.	72.0	22.8	15.8	14.5	16.8
28	21.3	27.3	27.3	19.4	26.6	190.	258.	72.0	23.4	15.8	14.5	17.3
29	23.2	26.6	26.6	19.4	-----	191.	246.	74.4	23.9	17.8	14.0	17.3
30	25.2	25.9	27.3	19.4	-----	196.	236.	73.2	27.2	18.3	14.0	17.8
31	25.2	-----	26.6	19.4	-----	210.	-----	69.6	-----	17.8	13.6	-----
Maks.	26.6	33.8	33.8	30.9	26.6	210.	466.	464.	78.0	48.0	18.3	17.8
Min.	17.2	24.6	24.6	19.4	19.4	28.0	212.	67.2	22.8	15.8	12.0	12.8
Ortalama	20.9	28.0	27.1	21.4	19.9	92.5	301.	222.	41.9	26.5	14.9	14.4
LT/SN/Km2	2.03	2.72	2.64	2.08	1.94	9.01	29.3	21.6	4.08	2.58	1.45	1.40
AKIM mm.	5.44	7.06	7.06	5.58	4.69	24.1	75.9	57.9	10.6	6.90	3.88	3.63
MİL. M3	55.9	72.5	72.5	57.3	48.1	248.	779.	595.	109.	70.9	39.8	37.2

SU YILI (2006) YILLIK TOPLAM AKIM 2185.20 MİLYON M3 213 MM. 6.7 LT/SN/Km2

24. Aras Havzasi

D24A069 SARIKAMIŞ S. YAĞBASAN

YERİ : **KARS SARIKAMIŞ YOLU ÜZERİNDE YAĞBASAN KÖYÜNDEDIR.**
42°38'54" Doğu - 40°22'14" Kuzey

YAĞIŞ ALANI : **114,94 km2** **YAKLAŞIK KOT : 2007 m**

GÖZLEM SÜRESİ : **01.10.1985 - 30.09.2006**

ORTALAMA AKIMLAR : **Gözlem süresinde 1.103 m3/sn. (20 Yıllık) 2006 Su yılında 1.837 m3/sn.**

ANLIK EN ÇOK VE EN AZ AKIMLAR:

2006 Su yılında anlık ençok akım	:	**10.5**	**m3/sn**	**25.04.2006**
2006 Su yılında anlık enaz akım	:	**0.022**	**m3/sn**	**09.08.2006**
Gözlem süresinde anlık ençok akım	:	**27.0**	**m3/sn**	**05.06.1995**
Gözlem süresinde anlık enaz akım	:	**0.001**	**m3/sn**	**01.01.2000**

Akımlar 01 Ekim 2005 'den 30 Eylül 2006' a kadar m3/sn olarak

Gün	Ekim	Kasım	Aralık	Ocak	Şubat	Mart	Nisan	Mayıs	Haziran	Temmuz	Ağustos	Eylül
01	0.690	2.82	1.07	0.882	0.882	1.75	8.18	6.75	2.82	1.16	0.074	0.252
02	0.690	2.14	0.978	0.882	0.882	2.14	8.18	6.59	2.82	1.27	0.113	0.187
03	0.690	1.88	1.07	0.882	0.882	2.40	8.16	6.75	2.82	0.894	0.113	0.187
04	0.882	1.75	1.17	0.882	0.882	2.82	5.64	7.06	1.68	0.692	0.074	0.187
05	0.690	1.63	1.07	0.882	0.882	2.68	3.78	6.75	1.54	0.428	0.074	0.187
06	0.690	1.75	0.978	0.882	0.882	2.82	3.60	6.75	1.41	0.428	0.074	0.187
07	0.690	1.75	0.978	0.882	0.882	3.10	3.42	7.06	1.04	0.260	0.074	0.252
08	0.690	1.63	0.882	0.882	0.882	3.25	4.31	7.06	0.928	0.260	0.074	0.252
09	0.690	1.40	0.882	0.882	0.882	3.55	5.64	6.90	0.700	0.200	0.074	0.252
10	0.690	1.29	0.882	0.882	0.882	3.40	6.02	6.59	0.610	0.200	0.040	0.252
11	0.690	1.17	0.882	0.882	0.882	3.40	6.60	6.59	0.610	0.200	0.040	0.252
12	0.690	1.17	0.882	0.882	0.882	3.40	6.79	5.97	0.521	0.200	0.113	0.342
13	0.690	1.07	0.786	0.882	0.882	3.40	6.79	5.51	0.521	0.162	0.187	0.342
14	0.690	1.07	0.882	0.882	0.882	3.55	6.99	5.35	0.521	0.162	0.130	0.252
15	0.690	0.978	0.786	0.882	0.882	3.55	6.99	5.20	0.431	0.162	0.187	0.342
16	0.690	0.978	0.786	0.882	0.882	3.55	7.77	4.75	0.431	0.162	0.130	0.342
17	2.96	0.978	0.786	0.882	0.882	3.55	7.18	4.60	0.431	0.162	0.130	0.342
18	1.29	0.978	0.882	0.882	0.882	3.55	6.99	4.45	0.431	0.260	0.130	0.342
19	1.07	0.978	0.882	0.882	0.882	3.55	6.79	4.15	0.431	0.113	0.187	0.342
20	1.29	0.978	0.882	0.882	0.882	3.55	6.79	3.85	0.431	0.113	0.187	0.342
21	1.07	0.978	1.63	0.882	0.882	3.55	7.96	3.85	0.521	0.113	0.252	0.342
22	0.882	1.07	1.75	0.882	0.882	3.70	6.99	3.25	0.431	0.113	0.252	0.342
23	0.786	1.07	1.40	0.882	0.882	4.00	7.18	2.96	0.431	0.074	0.252	0.342
24	0.786	0.786	0.978	0.882	0.882	4.45	8.35	2.96	0.431	0.074	0.252	0.342
25	0.690	0.882	0.882	0.882	0.882	5.51	8.55	2.96	0.342	0.074	0.252	0.431
26	0.690	0.978	0.882	0.882	0.882	5.82	7.70	2.82	0.342	0.113	0.252	0.342
27	0.690	0.882	0.882	0.882	0.882	5.66	7.22	2.82	0.431	0.074	0.252	0.342
28	0.786	0.978	0.882	0.882	0.882	5.66	6.75	2.82	0.431	0.074	0.252	0.342
29	1.29	1.07	0.882	0.882	-----	5.66	6.59	2.82	0.814	0.113	0.252	0.342
30	1.29	1.17	0.882	0.882	-----	6.13	7.06	2.82	0.814	0.113	0.252	0.342
31	1.88	-----	0.882	0.882	-----	6.90	-----	2.82	-----	0.074	0.252	-----
Maks.	3.85	3.55	2.68	0.882	0.882	8.34	10.5	7.54	3.85	1.75	0.814	0.700
Min.	0.613	0.613	0.690	0.882	0.882	1.63	2.71	2.82	0.187	0.040	0.022	0.187
Ortalama	0.925	1.28	0.978	0.882	0.882	3.87	6.70	4.89	0.871	0.274	0.161	0.298
LT/SN/Km2	8.05	11.1	8.51	7.67	7.67	33.7	58.3	42.5	7.57	2.38	1.40	2.59
AKIM mm.	21.6	28.8	22.8	20.6	18.6	90.2	151.	114.	19.6	6.39	3.74	6.72
MİL. M3	2.48	3.30	2.62	2.36	2.13	10.4	17.4	13.1	2.26	0.734	0.430	0.773

SU YILI (2006) YILLIK TOPLAM AKIM 57.99 MİLYON M3 504 MM. 16.0 LT/SN/Km2

24. Aras Havzasi

D24A071 BÜYÜK D. BÜYÜKDERE

YERİ : **PASİNLERE 9 KM MESAFEDEKİ BÜYÜKDERE KÖYÜNÜN 1 KM MENBASINDADIR.**
41°37'2" Doğu - 40°3'28" Kuzey

YAĞIŞ ALANI : **127,90 km2** **YAKLAŞIK KOT : 1788 m**

GÖZLEM SÜRESİ : **01.05.1987 - 30.09.2006**

ORTALAMA AKIMLAR : **Gözlem süresinde 1.819 m3/sn. (18 Yıllık) 2006 Su yılında 1.814 m3/sn.**

ANLIK EN ÇOK VE EN AZ AKIMLAR:

2006 Su yılında anlık ençok akım	**:**	**13.9**	**m3/sn**	**24.04.2006**
2006 Su yılında anlık enaz akım	**:**	**0.138**	**m3/sn**	**10.08.2006**
Gözlem süresinde anlık ençok akım	**:**	**92.0**	**m3/sn**	**28.04.1990**
Gözlem süresinde anlık enaz akım	**:**	**0.021**	**m3/sn**	**20.12.1995**

11. Anahtar Eğrisi (Seviyeler cm olarak)

Seviye	Akım	Seviye	Akım	Seviye	Akım	Seviye	Akım
12	0.007	22	0.066	40	0.580	90	7.6
14	0.013	24	0.088	50	1.2	100	10.3
16	0.021	26	0.120	60	2.2	110	13.1
18	0.031	28	0.155	70	3.6	120	16.2
20	0.046	30	0.200	80	5.4	130	19.8

Akımlar 01 Ekim 2005 'den 30 Eylül 2006' a kadar m3/sn olarak

Gün	Ekim	Kasım	Aralık	Ocak	Şubat	Mart	Nisan	Mayıs	Haziran	Temmuz	Ağustos	Eylül
01	0.293	0.650	0.535	0.420	0.375	0.420	1.68	8.54	4.50	1.27	0.310	0.185
02	0.293	0.650	0.480	0.420	0.375	0.420	1.68	8.77	4.34	1.11	0.310	0.185
03	0.293	0.650	0.480	0.420	0.375	0.420	1.68	8.77	4.34	1.35	0.310	0.160
04	0.293	0.650	0.480	0.420	0.375	0.420	1.68	8.77	3.72	1.55	0.310	0.138
05	0.293	0.650	0.480	0.420	0.375	0.420	1.80	9.75	3.72	1.45	0.310	0.185
06	0.253	0.650	0.535	0.420	0.375	0.420	1.93	9.75	3.57	1.35	0.275	0.215
07	0.253	0.650	0.535	0.420	0.375	0.420	2.05	10.0	3.57	1.03	0.310	0.215
08	0.253	0.650	0.480	0.420	0.375	0.420	2.56	10.3	3.10	0.950	0.215	0.185
09	0.293	0.715	0.480	0.420	0.375	0.420	4.50	9.50	2.85	0.878	0.185	0.185
10	0.375	0.715	0.535	0.420	0.375	0.420	5.28	9.75	2.23	0.806	0.275	0.240
11	0.595	0.650	0.480	0.420	0.375	0.420	5.90	9.75	1.85	0.734	0.215	0.160
12	0.595	0.650	0.480	0.420	0.375	0.420	6.30	9.50	1.75	0.734	0.185	0.185
13	0.535	0.650	0.480	0.420	0.375	0.420	7.03	9.50	1.65	0.734	0.215	0.240
14	0.595	0.650	0.480	0.420	0.375	0.480	7.77	9.25	1.65	0.734	0.215	0.240
15	0.535	0.595	0.535	0.420	0.375	0.480	9.00	9.25	1.65	0.734	0.240	0.185
16	0.595	0.715	0.420	0.420	0.375	0.332	10.3	9.25	1.45	0.734	0.215	0.185
17	1.58	0.715	0.420	0.420	0.375	0.293	9.25	9.25	1.45	0.662	0.160	0.215
18	0.860	0.715	0.420	0.420	0.375	0.480	9.50	9.50	1.35	0.496	0.240	0.215
19	0.780	0.595	0.420	0.420	0.375	0.480	9.50	8.50	1.19	0.355	0.215	0.185
20	0.860	0.595	0.420	0.420	0.375	0.480	10.5	8.50	1.11	0.355	0.185	0.215
21	0.780	0.715	0.420	0.420	0.480	0.375	11.1	8.50	1.03	0.355	0.185	0.215
22	0.715	0.715	0.420	0.420	0.535	0.650	10.8	9.00	1.03	0.355	0.215	0.215
23	0.650	0.650	0.420	0.420	0.535	0.535	10.8	9.00	0.950	0.402	0.185	0.215
24	0.650	0.650	0.420	0.420	0.375	0.715	11.1	8.75	0.950	0.449	0.215	0.215
25	0.650	0.780	0.420	0.420	0.375	0.780	11.6	8.75	1.03	0.355	0.185	0.215
26	0.650	0.715	0.420	0.420	0.420	0.715	9.26	8.50	0.950	0.310	0.160	0.185
27	0.650	0.650	0.420	0.420	0.420	0.595	9.52	5.88	0.950	0.240	0.185	0.185
28	0.650	0.595	0.420	0.420	0.375	0.595	8.54	5.27	0.950	0.185	0.215	0.215
29	0.650	0.535	0.420	0.420	-----	0.715	8.08	4.65	0.950	0.402	0.185	0.215
30	0.650	0.480	0.420	0.420	-----	1.18	9.00	4.86	1.19	0.275	0.160	0.215
31	0.650	-----	0.420	0.420	-----	1.58	-----	4.86	-----	0.310	0.215	-----
Maks.	2.69	0.780	0.535	0.420	0.535	1.58	13.9	12.5	6.09	3.10	0.449	0.275
Min.	0.253	0.480	0.420	0.420	0.375	0.293	1.68	4.03	0.878	0.160	0.138	0.138
Ortalama	0.573	0.655	0.458	0.420	0.393	0.546	6.99	8.52	2.03	0.699	0.226	0.200
LT/SN/Km2	4.48	5.12	3.58	3.28	3.08	4.27	54.6	66.6	15.9	5.46	1.77	1.57
AKIM mm.	12.0	13.3	9.59	8.80	7.44	11.4	142.	178.	41.2	14.6	4.73	4.06
MİL. M3	1.54	1.70	1.23	1.12	0.952	1.46	18.1	22.8	5.27	1.87	0.605	0.519

SU YILI (2006) YILLIK TOPLAM AKIM 57.17 MİLYON M3 447 MM. 14.2 LT/SN/Km2

24. Aras Havzasi

D24A073 KATRANLİ Ç. BÖLÜKBASİ

YERİ : **KARS İLI SELIM ILÇESI 10 KM MESAFEDEKI BÖLÜKBAŞI KÖYÜNDEDIR.**
42°41'16" Doğu - 40°29'8" Kuzey

YAĞIŞ ALANI : **140,00 km2** **YAKLAŞIK KOT : 1907 m**

GÖZLEM SÜRESİ : **01.10.1987 - 30.09.2006**

ORTALAMA AKIMLAR : **Gözlem süresinde 0.789 m3/sn. (18 Yıllık) 2006 Su yılında 0.686 m3/sn.**

ANLIK EN ÇOK VE EN AZ AKIMLAR:

2006 Su yılında anlık ençok akım	:	**3.55**	**m3/sn**	**29.04.2006**
2006 Su yılında anlık enaz akım	:	**0.038**	**m3/sn**	**13.05.2006**
Gözlem süresinde anlık ençok akım	:	**15.5**	**m3/sn**	**24.03.1990**
Gözlem süresinde anlık enaz akım	:	**0.011**	**m3/sn**	**12.03.1999**

Akımlar 01 Ekim 2005 'den 30 Eylül 2006' a kadar m3/sn olarak

Gün	Ekim	Kasım	Aralık	Ocak	Şubat	Mart	Nisan	Mayıs	Haziran	Temmuz	Ağustos	Eylül
01	0.533	1.25	0.612	0.454	0.454	0.454	1.71	3.40	0.612	0.962	0.304	0.247
02	0.612	1.25	0.533	0.454	0.454	0.454	0.962	2.56	0.612	1.83	0.454	0.247
03	0.612	1.06	0.612	0.454	0.454	0.454	0.770	2.56	0.612	1.25	0.375	0.247
04	0.454	0.962	0.691	0.454	0.454	0.454	0.533	2.97	0.612	1.15	0.375	0.247
05	0.454	0.962	0.612	0.454	0.454	0.454	0.691	2.43	0.612	1.37	0.332	0.289
06	0.375	1.15	0.533	0.454	0.454	0.454	0.612	2.29	0.612	1.44	0.332	0.289
07	0.533	1.25	0.533	0.454	0.454	0.454	0.612	2.16	0.612	0.460	0.332	0.289
08	0.533	1.15	0.533	0.454	0.454	0.454	1.06	2.02	0.612	0.356	0.332	0.289
09	0.533	0.962	0.612	0.454	0.454	0.454	2.42	2.16	0.533	0.304	0.289	0.289
10	0.454	0.770	0.533	0.454	0.454	0.454	2.42	2.29	0.533	0.252	0.247	0.289
11	0.375	0.691	0.533	0.454	0.454	0.454	0.866	2.29	0.533	0.252	0.247	0.289
12	0.375	0.691	0.533	0.454	0.454	0.454	0.612	2.70	0.533	0.252	0.289	0.289
13	0.454	0.691	0.612	0.454	0.454	0.454	0.375	2.16	0.454	0.200	0.289	0.332
14	0.533	0.691	0.691	0.454	0.454	0.454	0.375	2.43	0.332	0.200	0.247	0.289
15	0.533	0.612	0.962	0.454	0.454	0.454	0.454	2.56	0.289	0.252	0.204	0.332
16	0.533	0.691	1.25	0.454	0.454	0.454	1.83	2.43	0.289	0.252	0.247	0.332
17	1.37	0.691	0.691	0.454	0.454	0.454	1.25	2.43	0.332	0.304	0.247	0.332
18	0.691	0.691	0.612	0.454	0.454	0.454	1.15	2.43	0.332	0.356	0.247	0.332
19	0.612	0.612	0.454	0.454	0.454	0.454	1.06	2.29	0.332	0.252	0.289	0.332
20	0.691	0.612	0.454	0.454	0.454	0.454	1.06	2.29	0.454	0.252	0.332	0.289
21	0.612	0.612	0.454	0.454	0.454	0.454	1.15	1.98	0.375	0.252	0.289	0.332
22	0.533	0.770	0.454	0.454	0.454	0.454	1.48	1.25	0.332	0.252	0.289	0.332
23	0.533	0.770	0.454	0.454	0.454	0.454	1.15	1.06	0.375	0.252	0.289	0.375
24	0.533	1.60	0.454	0.454	0.454	0.454	1.15	0.866	0.454	0.252	0.289	0.375
25	0.533	1.60	0.454	0.454	0.454	0.454	1.25	0.770	0.375	0.252	0.332	0.375
26	0.533	1.71	0.454	0.454	0.454	0.454	3.01	0.691	0.375	0.252	0.289	0.375
27	0.533	0.533	0.454	0.454	0.454	0.454	2.56	0.691	0.375	0.252	0.289	0.332
28	0.533	0.533	0.454	0.454	0.454	0.454	2.29	0.691	0.375	0.200	0.247	0.332
29	0.691	0.533	0.454	0.454	-----	0.454	3.55	0.691	0.454	0.252	0.247	0.375
30	0.962	0.691	0.454	0.454	-----	0.454	2.56	0.612	0.866	0.252	0.247	0.375
31	0.962	-----	0.454	0.454	-----	0.454	-----	0.612	-----	0.200	0.247	-----
Maks.	2.12	2.71	2.12	0.454	0.454	0.454	3.55	3.47	2.57	2.70	0.850	0.375
Min.	0.375	0.454	0.332	0.454	0.454	0.454	0.375	0.038	0.247	0.172	0.204	0.204
Ortalama	0.588	0.893	0.567	0.454	0.454	0.454	1.37	1.90	0.473	0.471	0.292	0.315
LT/SN/Km2	4.20	6.38	4.05	3.24	3.24	3.24	9.76	13.5	3.38	3.37	2.09	2.25
AKIM mm.	11.2	16.5	10.9	8.69	7.85	8.69	25.3	36.3	8.76	9.02	5.59	5.83
MİL. M3	1.57	2.31	1.52	1.22	1.10	1.22	3.54	5.08	1.23	1.26	0.783	0.816

SU YILI (2006) YILLIK TOPLAM AKIM 21.65 MİLYON M3 155 MM. 4.9 LT/SN/Km2

DSI
24. Aras Havzasi
D24A074 ÇUBUK D. ÇATAK

YER :KARS - SARIKAMIŞ YOLU ÜZERİNDEKİ ÇATAK KÖYÜNDEDİR.
:42°40' D-40°24' K

YAĞIŞ ALANI :53.60 km2 **YAKLAŞIK KOT** 1930 m.
GÖZLEM SÜRESİ : 01.10.1987 - 30.09.2005 **GÖZLEM SÜR. ORT. AKIM** **1.853** m3/sn

AYLIK TOPLAM AKIMLAR (HM3) (milm3)

YIL	EKİ	KAS	ARA	OCA	ŞUB	MAR	NİS	MAY	HAZ	TEM	AĞU	EYL	TOP
2003	0.288	0.165	0.651	0.723	0.641	0.825	6.42	10.1	5.58	3.34	2.06	1.43	32.2
2004	1.65	1.39	1.57	1.71	1.60	2.21	5.48	11.9	5.06	1.53	0.148	0.101	34.4
2005	0.206	0.338	0.090	0.067	0.060	1.29	28.9	11.0	3.37	0.875	0.354	0.650	47.2

24. Aras Havzasi

D24A074 ÇUBUK D. ÇATAK

YERİ : **KARS - SARIKAMIŞ YOLU ÜZERİNDEKİ ÇATAK KÖYÜNDEDİR.**
42°40'46" Doğu - 40°24'18" Kuzey

YAĞIŞ ALANI : **53,60 km2** **YAKLAŞIK KOT : 1930 m**

GÖZLEM SÜRESİ : **01.10.1987 - 30.09.2006**

ORTALAMA AKIMLAR : **Gözlem süresinde 1.676 m3/sn. (7 Yıllık) 2006 Su yılında 1.853 m3/sn.**

ANLIK EN ÇOK VE EN AZ AKIMLAR:

2006 Su yılında anlık ençok akım	:	**15.8**	**m3/sn**	**01.04.2006**
2006 Su yılında anlık enaz akım	:	**0.041**	**m3/sn**	**12.08.2006**
Gözlem süresinde anlık ençok akım	:	**18.1**	**m3/sn**	**26.04.2005**
Gözlem süresinde anlık enaz akım	:	**0.012**	**m3/sn**	**29.01.2001**

Akımlar 01 Ekim 2005 'den 30 Eylül 2006' a kadar m3/sn olarak

Gün	Ekim	Kasım	Aralık	Ocak	Şubat	Mart	Nisan	Mayıs	Haziran	Temmuz	Ağustos	Eylül
01	0.355	0.439	2.39	2.39	2.39	3.07	10.9	4.04	0.662	0.196	0.091	0.041
02	0.283	0.439	2.39	2.39	2.39	3.07	4.04	3.80	0.569	0.196	0.091	0.121
03	0.355	0.355	2.39	2.39	2.39	3.73	2.84	3.56	0.405	0.196	0.091	0.121
04	0.283	0.355	2.39	2.39	2.39	4.06	2.36	3.32	0.569	0.196	0.091	0.121
05	0.355	0.439	2.39	2.39	2.39	4.39	2.12	3.08	0.569	0.156	0.091	0.091
06	0.439	0.355	2.39	2.39	2.39	4.06	2.12	3.08	0.475	0.239	0.091	0.091
07	0.439	0.355	2.39	2.39	2.39	4.39	2.60	3.08	0.475	0.196	0.091	0.091
08	0.439	0.355	2.39	2.39	2.39	4.39	2.84	3.08	0.475	0.156	0.091	0.091
09	0.525	0.439	2.39	2.39	2.39	3.73	4.04	3.08	0.405	0.156	0.064	0.091
10	0.439	0.525	2.39	2.39	2.39	3.40	4.46	2.84	0.405	0.239	0.064	0.091
11	0.283	0.630	2.39	2.39	2.39	3.40	4.88	2.60	0.405	0.121	0.064	0.121
12	0.145	0.850	2.39	2.39	2.39	4.06	5.30	2.36	0.347	0.121	0.064	0.121
13	0.145	0.630	2.39	2.39	2.39	4.06	6.15	2.12	0.347	0.091	0.041	0.121
14	0.145	0.525	2.39	2.39	2.39	4.06	6.57	2.36	0.347	0.091	0.064	0.156
15	0.145	0.733	2.39	2.39	2.39	2.84	6.99	1.88	0.347	0.091	0.064	0.196
16	0.145	0.525	2.39	2.39	2.39	3.07	6.99	1.64	0.290	0.091	0.064	0.121
17	0.525	1.77	2.39	2.39	2.39	4.06	7.41	1.50	0.290	0.121	0.064	0.196
18	0.283	2.61	2.39	2.39	2.39	3.73	7.83	1.50	0.290	0.156	0.064	0.121
19	0.283	2.61	2.39	2.39	2.39	3.40	9.56	1.36	0.239	0.091	0.091	0.121
20	0.439	2.84	2.39	2.39	2.39	3.40	10.2	1.36	0.239	0.091	0.091	0.121
21	0.525	2.84	2.39	2.39	2.39	3.73	10.9	1.22	0.239	0.091	0.091	0.156
22	0.355	2.84	2.39	2.39	2.39	3.73	10.2	1.22	0.239	0.091	0.091	0.156
23	0.439	2.61	2.39	2.39	2.39	3.40	8.91	1.22	0.239	0.091	0.064	0.121
24	0.355	2.84	2.39	2.39	2.39	3.73	7.41	1.08	0.239	0.091	0.091	0.121
25	0.525	3.07	2.39	2.39	2.39	4.39	6.15	1.08	0.196	0.091	0.091	0.121
26	0.439	2.39	2.39	2.39	2.39	3.73	6.15	0.943	0.121	0.091	0.091	0.156
27	0.439	2.84	2.39	2.39	2.39	5.06	6.15	0.943	0.121	0.091	0.091	0.121
28	0.355	2.39	2.39	2.39	2.39	9.33	6.57	0.943	0.121	0.091	0.091	0.121
29	0.439	2.61	2.39	2.39	-----	9.33	4.88	0.756	0.156	0.121	0.091	0.121
30	0.439	2.61	2.39	2.39	-----	9.33	4.04	0.849	0.156	0.091	0.064	0.121
31	0.439	-----	2.39	2.39	-----	10.8	-----	0.849	-----	0.091	0.064	-----
Maks.	7.86	4.06	2.39	2.39	2.39	14.7	15.8	6.15	1.64	0.475	0.196	0.239
Min.	0.145	0.355	2.39	2.39	2.39	1.77	2.12	0.475	0.121	0.064	0.041	0.041
Ortalama	0.361	1.49	2.39	2.39	2.39	4.55	6.05	2.02	0.333	0.130	0.079	0.122
LT/SN/Km2	6.74	27.9	44.6	44.6	44.6	84.8	113.	37.8	6.20	2.42	1.47	2.28
AKIM mm.	18.1	72.2	119.	119.	108.	227.	293.	101.	16.1	6.48	3.94	5.90
MİL. M3	0.968	3.87	6.40	6.40	5.78	12.2	15.7	5.42	0.862	0.348	0.211	0.316

SU YILI (2006) YILLIK TOPLAM AKIM 58.48 MİLYON M3 1091 MM. 34.6 LT/SN/Km2

24. Aras Havzasi

D24A081 ÇAMLIKALE D. DÖNERTAŞ

YERİ : **ERZURUM İLİ HORASAN İLÇESİ DÖNERTAŞ KÖYÜNDEDİR.**
42°7'49" Doğu - 40°13'5" Kuzey

YAĞIŞ ALANI : **49,60 km2** **YAKLAŞIK KOT : 1910 m**

GÖZLEM SÜRESİ : **01.10.1991 - 30.09.2006**

ORTALAMA AKIMLAR : **Gözlem süresinde 1.015 m3/sn. (8 Yıllık) 2006 Su yılında 0.709 m3/sn.**

ANLIK EN ÇOK VE EN AZ AKIMLAR:

2006 Su yılında anlık ençok akım	**:**	**14.4**	**m3/sn**	**12.04.2006**
2006 Su yılında anlık enaz akım	**:**	**0.020**	**m3/sn**	**04.02.2006**
Gözlem süresinde anlık ençok akım	**:**	**47.5**	**m3/sn**	**20.07.1992**
Gözlem süresinde anlık enaz akım	**:**	**0.000**	**m3/sn**	**11.10.2003**

İstasyon için kullanılmış anahtar bulunamadı.

Akımlar 01 Ekim 2005 'den 30 Eylül 2006' a kadar m3/sn olarak

Gün	Ekim	Kasım	Aralık	Ocak	Şubat	Mart	Nisan	Mayıs	Haziran	Temmuz	Ağustos	Eylül
01	0.125	0.325	0.185	0.150	0.125	0.185	0.692	2.64	0.734	0.630	0.254	0.179
02	0.125	0.222	0.185	0.150	0.102	0.185	0.876	2.64	0.734	0.630	0.254	0.179
03	0.125	0.222	0.185	0.125	0.125	0.222	1.09	2.82	0.734	0.510	0.254	0.179
04	0.150	0.185	0.222	0.102	0.102	0.185	1.30	3.23	0.734	0.630	0.254	0.179
05	0.150	0.185	0.222	0.102	0.125	0.185	1.30	2.82	0.630	0.630	0.254	0.179
06	0.125	0.185	0.222	0.102	0.125	0.222	1.30	3.23	0.630	0.510	0.217	0.179
07	0.125	0.222	0.185	0.125	0.125	0.222	1.30	3.46	0.630	0.450	0.217	0.179
08	0.125	0.222	0.185	0.125	0.125	0.222	1.78	3.23	0.570	0.450	0.217	0.179
09	0.125	0.222	0.185	0.125	0.125	0.185	3.92	2.82	0.510	0.390	0.217	0.179
10	0.125	0.185	0.185	0.125	0.125	0.222	4.84	2.64	0.510	0.390	0.217	0.179
11	0.125	0.222	0.185	0.125	0.125	0.222	5.92	2.28	0.450	0.450	0.217	0.179
12	0.125	0.185	0.185	0.125	0.125	0.222	7.47	2.28	0.450	0.390	0.179	0.179
13	0.102	0.222	0.150	0.102	0.125	0.222	7.47	2.28	0.450	0.330	0.179	0.217
14	0.102	0.185	0.150	0.125	0.125	0.222	7.47	2.28	0.450	0.330	0.179	0.217
15	0.102	0.185	0.150	0.125	0.150	0.222	8.73	2.28	0.450	0.330	0.179	0.217
16	0.125	0.150	0.150	0.102	0.102	0.222	9.30	2.28	0.450	0.330	0.179	0.217
17	0.614	0.150	0.150	0.102	0.102	0.222	6.60	2.28	0.390	0.292	0.179	0.217
18	0.222	0.185	0.150	0.102	0.125	0.222	6.25	2.28	0.390	0.254	0.179	0.217
19	0.185	0.185	0.150	0.102	0.125	0.222	5.55	1.94	0.390	0.254	0.179	0.217
20	0.185	0.185	0.150	0.102	0.150	0.222	5.20	1.61	0.390	0.254	0.179	0.217
21	0.185	0.185	0.150	0.102	0.150	0.185	6.25	1.61	0.390	0.217	0.217	0.217
22	0.185	0.185	0.150	0.102	0.150	0.222	4.15	1.50	0.390	0.254	0.217	0.217
23	0.185	0.150	0.150	0.102	0.150	0.222	3.02	1.27	0.390	0.254	0.217	0.217
24	0.222	0.185	0.125	0.080	0.150	0.265	4.15	1.15	0.390	0.254	0.217	0.217
25	0.150	0.185	0.125	0.102	0.150	0.325	5.07	1.05	0.390	0.254	0.217	0.217
26	0.222	0.185	0.125	0.125	0.150	0.325	4.15	1.05	0.390	0.254	0.217	0.217
27	0.185	0.185	0.150	0.125	0.150	0.325	3.23	0.942	0.390	0.254	0.217	0.217
28	0.185	0.185	0.150	0.125	0.185	0.380	2.46	0.838	0.450	0.254	0.217	0.217
29	0.222	0.185	0.150	0.125	-----	0.380	2.10	0.942	0.450	0.254	0.179	0.217
30	0.185	0.222	0.150	0.125	-----	0.458	2.64	0.838	0.450	0.254	0.217	0.254
31	0.185	-----	0.150	0.125	-----	0.536	-----	0.734	-----	0.254	0.179	-----
Maks.	3.69	0.458	0.265	0.222	0.265	0.770	14.4	5.30	0.734	5.33	0.292	0.450
Min.	0.102	0.125	0.080	0.063	0.020	0.102	0.536	0.325	0.330	0.179	0.179	0.179
Ortalama	0.171	0.196	0.165	0.116	0.132	0.254	4.19	2.04	0.492	0.361	0.209	0.203
LT/SN/Km2	3.45	3.95	3.32	2.33	2.66	5.12	84.4	41.1	9.92	7.28	4.22	4.09
AKIM mm.	9.23	10.2	8.89	6.24	6.43	13.7	219.	110.	25.7	19.5	11.3	10.6
MİL. M3	0.458	0.508	0.441	0.309	0.319	0.681	10.8	5.46	1.27	0.967	0.561	0.526

SU YILI (2006) YILLIK TOPLAM AKIM 22.30 MİLYON M3 450 MM. 14.3 LT/SN/Km2

24. Aras Havzasi

D24A083 SÜNGÜTAŞ D. ÇERMİK

YERİ : **ERZURUM İLİ HORASAN İLÇESİNE BAĞLI ÇERMİK KÖYÜNDEDİR.**
42°14'55" Doğu - 40°7'35" Kuzey

YAĞIŞ ALANI : **486,30 km2** **YAKLAŞIK KOT : 1636 m**

GÖZLEM SÜRESİ : **01.10.1992 - 30.09.2006**

ORTALAMA AKIMLAR : **Gözlem süresinde 4.210 m3/sn. (11 Yıllık) 2006 Su yılında 4.395 m3/sn.**

ANLIK EN ÇOK VE EN AZ AKIMLAR:

2006 Su yılında anlık ençok akım	:	**42.8**	**m3/sn**	**16.04.2006**
2006 Su yılında anlık enaz akım	:	**0.550**	**m3/sn**	**25.06.2006**
Gözlem süresinde anlık ençok akım	:	**91.0**	**m3/sn**	**13.05.1993**
Gözlem süresinde anlık enaz akım	:	**0.205**	**m3/sn**	**20.02.2000**

8. Anahtar Eğrisi (Seviyeler cm olarak)

Seviye	Akım	Seviye	Akım	Seviye	Akım	Seviye	Akım
25	0.620	55	4.2	140	26.4	190	46.0
27	0.750	70	7.0	150	29.7	200	50.8
29	0.915	90	11.7	160	33.2	210	55.6
35	1.4	110	17.2	170	37.0	220	60.4
45	2.6	130	23.3	180	41.2	230	65.2

Akımlar 01 Ekim 2005 'den 30 Eylül 2006' a kadar m3/sn olarak

Gün	Ekim	Kasım	Aralık	Ocak	Şubat	Mart	Nisan	Mayıs	Haziran	Temmuz	Ağustos	Eylül
01	1.25	5.13	1.68	1.68	1.68	1.36	16.2	21.9	2.47	2.11	1.10	0.900
02	1.10	3.51	1.68	1.68	1.68	1.36	17.2	20.8	2.11	2.47	1.10	0.900
03	1.10	2.84	1.68	1.68	1.68	1.52	17.0	21.3	2.65	2.89	1.10	0.900
04	1.25	2.63	1.68	1.68	1.68	1.68	15.5	23.5	2.29	3.61	1.10	0.900
05	1.25	2.42	1.68	1.68	1.68	1.36	10.8	21.3	2.29	2.65	1.10	1.00
06	1.25	2.42	1.68	1.68	1.68	1.52	10.8	22.4	1.93	2.11	1.10	1.10
07	1.25	2.42	1.68	1.68	1.20	1.68	9.48	24.2	1.62	1.75	1.10	1.36
08	1.25	2.42	1.68	1.68	1.09	1.84	12.1	24.2	1.62	1.62	1.00	1.36
09	1.25	2.21	1.68	1.68	1.09	2.42	19.7	23.5	1.49	1.62	1.00	1.36
10	1.10	2.00	1.52	1.68	1.09	2.42	21.9	21.3	1.36	1.49	1.00	1.36
11	1.10	1.84	1.68	1.68	1.09	2.00	24.2	18.6	1.23	1.49	1.00	1.49
12	1.10	1.68	1.52	1.68	1.09	1.84	26.1	16.5	1.10	1.36	1.00	1.49
13	1.10	1.68	1.20	1.68	1.09	2.00	26.8	15.0	1.00	1.36	1.00	1.49
14	1.10	1.84	1.36	1.68	1.20	2.00	27.4	13.5	1.00	1.23	1.00	1.49
15	1.10	1.84	1.36	1.68	1.20	2.63	30.7	11.7	0.900	1.23	1.00	1.36
16	1.10	1.84	1.68	1.68	1.09	2.42	37.2	9.48	0.900	1.23	1.00	1.49
17	2.84	1.68	1.68	1.68	1.09	2.63	33.9	9.04	0.800	1.23	1.00	1.36
18	1.20	1.68	1.52	1.68	1.20	2.84	29.4	8.60	0.700	1.23	1.00	1.36
19	0.768	1.68	1.68	1.68	1.52	3.05	25.5	7.28	0.700	1.23	1.00	1.36
20	0.984	1.68	1.68	1.68	1.68	2.63	23.5	6.29	0.700	1.23	1.00	1.36
21	0.876	1.84	1.68	1.68	1.68	2.42	28.1	6.62	0.800	1.10	1.00	1.36
22	0.768	2.00	1.68	1.68	1.68	2.63	26.1	5.63	0.800	1.10	1.10	1.36
23	0.660	1.52	1.68	1.68	1.68	2.63	26.1	4.72	0.800	1.10	1.36	1.36
24	1.20	1.36	1.68	1.68	1.68	3.28	28.7	4.14	0.800	1.10	1.10	1.36
25	1.20	1.52	1.68	1.68	1.68	5.13	33.9	3.61	0.610	1.10	1.00	1.49
26	1.20	1.68	1.36	1.68	1.68	6.37	31.3	2.89	0.610	1.10	1.00	1.49
27	1.20	1.68	1.68	1.68	1.36	6.68	28.1	3.61	0.610	1.10	1.10	1.49
28	1.09	1.68	1.68	1.68	1.20	7.30	23.5	4.14	1.00	1.10	1.10	1.49
29	2.00	1.68	1.84	1.68	-----	8.06	20.2	3.85	2.47	1.10	1.10	1.49
30	2.00	1.68	1.84	1.68	-----	9.20	26.8	3.13	1.93	1.10	1.00	1.49
31	4.20	-----	1.84	1.84	-----	11.6	-----	2.89	-----	1.10	0.900	-----
Maks.	9.20	6.37	2.21	2.21	2.21	17.7	42.8	32.0	5.63	8.27	1.75	1.75
Min.	0.660	1.09	1.09	1.68	0.876	0.984	8.27	2.29	0.550	1.10	0.700	0.900
Ortalama	1.32	2.07	1.63	1.69	1.41	3.44	23.6	12.4	1.31	1.52	1.05	1.33
LT/SN/Km2	2.71	4.26	3.36	3.47	2.90	7.06	48.5	25.6	2.69	3.13	2.15	2.73
AKIM mm.	7.26	11.0	9.00	9.28	7.01	18.9	126.	68.5	6.98	8.39	5.77	7.07
MİL. M3	3.53	5.36	4.38	4.51	3.41	9.20	61.2	33.3	3.39	4.08	2.80	3.44

SU YILI (2006) YILLIK TOPLAM AKIM 138.60 MİLYON M3 285 MM. 9.0 LT/SN/Km2

24. Aras Havzasi

D24A084 YARBOĞAZ D. YARBOĞAZ

YERİ : **ERZURUM AĞRI YOLUNUN 100 KM SİNDEN SAĞA AYRILAN YOLUN 3 KM SİNDEKİ YARBAĞAZ KÖYÜNÜN İÇERİSİNDEDİR.**
42°13'5" Doğu - 39°57'6" Kuzey

YAĞIŞ ALANI : **101,10 km2** **YAKLAŞIK KOT : 1697 m**

GÖZLEM SÜRESİ : **01.10.1991 - 30.06.2006**

ORTALAMA AKIMLAR : **Gözlem süresinde 0.000 m3/sn. (0 Yıllık) 2006 Su yılında ---- m3/sn.**

ANLIK EN ÇOK VE EN AZ AKIMLAR:

2006 Su yılında anlık ençok akım : ----- m3/sn

2006 Su yılında anlık enaz akım : ----- m3/sn

Gözlem süresinde anlık ençok akım : ----- m3/sn -----

Gözlem süresinde anlık enaz akım : ----- m3/sn -----

İstasyon için kullanılmış anahtar bulunamadı.

Akımlar 01 Ekim 2005 'den 30 Eylül 2006' a kadar m3/sn olarak

Gün	Ekim	Kasım	Aralık	Ocak	Şubat	Mart	Nisan	Mayıs	Haziran	Temmuz	Ağustos	Eylül
01	0.310	0.640	0.640	0.820	0.820	0.640	1.76	3.30	0.200	-----	-----	-----
02	0.310	0.530	0.640	0.820	0.820	0.640	1.58	2.90	0.310	-----	-----	-----
03	0.310	0.530	0.640	0.820	0.820	0.710	1.58	3.10	0.380	-----	-----	-----
04	0.310	0.530	0.640	0.820	0.820	0.710	1.58	3.30	0.252	-----	-----	-----
05	0.310	0.530	0.640	0.820	0.820	0.710	1.32	1.76	0.252	-----	-----	-----
06	0.310	0.530	0.640	0.820	0.820	0.820	1.32	2.50	0.200	-----	-----	-----
07	0.310	0.530	0.640	0.820	0.710	0.820	1.32	2.32	0.155	-----	-----	-----
08	0.310	0.530	0.640	0.820	0.640	0.950	1.58	2.32	0.155	-----	-----	-----
09	0.310	0.530	0.640	0.820	0.530	1.18	2.13	2.13	0.118	-----	-----	-----
10	0.310	0.530	0.640	0.820	0.530	1.05	2.32	1.76	0.118	-----	-----	-----
11	0.310	0.530	0.640	0.820	0.440	1.05	2.70	1.45	0.088	-----	-----	-----
12	0.310	0.530	0.640	0.820	0.440	1.05	3.10	1.45	0.065	-----	-----	-----
13	0.310	0.530	0.640	0.820	0.530	1.05	2.70	1.32	0.065	-----	-----	-----
14	0.310	0.640	0.640	0.820	0.530	1.05	3.10	1.32	0.088	-----	-----	-----
15	0.310	0.640	0.820	0.820	0.530	0.820	2.32	1.18	0.065	-----	-----	-----
16	0.310	0.640	0.640	0.820	0.530	0.640	2.70	1.05	0.046	-----	-----	-----
17	0.310	0.530	0.640	0.820	0.640	0.640	2.32	1.18	0.065	-----	-----	-----
18	0.310	0.640	0.640	0.820	0.710	0.640	2.70	1.05	0.065	-----	-----	-----
19	0.310	0.530	0.640	0.820	0.710	0.640	2.13	1.05	0.065	-----	-----	-----
20	0.380	0.530	0.640	0.820	0.710	0.640	2.32	0.950	0.065	-----	-----	-----
21	0.310	0.530	0.640	0.820	0.710	0.640	5.80	1.05	0.046	-----	-----	-----
22	0.310	0.530	0.640	0.820	0.710	0.640	3.10	0.950	0.046	-----	-----	-----
23	0.310	0.530	0.640	0.820	0.710	0.640	2.32	0.820	0.065	-----	-----	-----
24	0.252	0.530	0.640	0.820	0.710	0.640	4.16	0.820	0.046	-----	-----	-----
25	0.252	0.710	0.640	0.820	0.710	0.820	5.56	0.710	0.065	-----	-----	-----
26	0.252	0.640	0.710	0.820	0.710	1.05	4.60	0.640	0.118	-----	-----	-----
27	0.252	0.640	0.820	0.820	0.710	1.05	3.72	0.440	0.200	-----	-----	-----
28	0.252	0.640	0.820	0.820	0.710	1.18	2.70	0.380	0.440	-----	-----	-----
29	0.440	0.640	0.820	0.820	-----	1.05	2.32	0.380	0.252	-----	-----	-----
30	0.950	0.640	0.820	0.820	-----	1.05	3.94	0.310	0.200	-----	-----	-----
31	0.640	-----	0.820	0.820	-----	1.32	-----	0.252	-----	-----	-----	-----
Maks.	2.32	1.18	1.05	0.820	1.32	2.32	19.3	6.55	1.32	--	--	--
Min.	0.065	0.530	0.530	0.820	0.380	0.380	0.710	0.155	0.046	--	--	--
Ortalama	0.338	0.573	0.677	0.820	0.671	0.856	2.69	1.42	0.143	--	--	--
LT/SN/Km2	3.35	5.66	6.70	8.11	6.63	8.46	26.6	14.1	1.42	--	--	--
AKIM mm.	8.96	14.7	17.9	21.7	16.0	22.7	69.1	37.7	3.67	--	--	--
MİL. M3	0.906	1.48	1.81	2.20	1.62	2.29	6.98	3.81	0.371	--	--	--

SU YILI (2006)

24. Aras Havzasi

D24A085 KARAYAZI D. KARASU KÖYÜ

YERİ : **ERZURUM İLİ KARAYAZI İLÇESİNE BAĞLI KARASU KÖYÜNDEDİR.**
42°0'11" Doğu - 39°42'17" Kuzey

YAĞIŞ ALANI : **150,00 km2** **YAKLAŞIK KOT : 2128 m**

GÖZLEM SÜRESİ : **01.10.1991 - 30.09.2006**

ORTALAMA AKIMLAR : **Gözlem süresinde 1.492 m3/sn. (9 Yıllık) 2006 Su yılında 1.989 m3/sn.**

ANLIK EN ÇOK VE EN AZ AKIMLAR:

2006 Su yılında anlık ençok akım	**:**	**51.5**	**m3/sn**	**13.04.2006**
2006 Su yılında anlık enaz akım	**:**	**0.151**	**m3/sn**	**01.09.2006**
Gözlem süresinde anlık ençok akım	**:**	**51.5**	**m3/sn**	**13.04.2006**
Gözlem süresinde anlık enaz akım	**:**	**0.005**	**m3/sn**	**16.08.2000**

5. Anahtar Eğrisi (Seviyeler cm olarak)

Seviye	Akım	Seviye	Akım	Seviye	Akım	Seviye	Akım
16	0.005	26	0.034	70	2.2	160	32.8
18	0.007	28	0.048	90	5.4	170	38.3
20	0.011	30	0.065	110	10.8	180	44.0
22	0.016	40	0.245	130	18.0	190	50.2
24	0.024	50	0.580	150	27.3	200	56.5

Akımlar 01 Ekim 2005 'den 30 Eylül 2006' a kadar m3/sn olarak

Gün	Ekim	Kasım	Aralık	Ocak	Şubat	Mart	Nisan	Mayıs	Haziran	Temmuz	Ağustos	Eylül
01	0.221	0.221	0.323	0.539	0.539	0.539	4.18	11.5	0.704	0.416	0.245	0.174
02	0.221	0.245	0.297	0.539	0.539	0.539	6.18	11.5	0.498	0.539	0.297	0.151
03	0.221	0.271	0.323	0.539	0.539	0.539	6.70	10.8	0.766	0.539	0.245	0.151
04	0.221	0.271	0.323	0.539	0.539	0.539	7.48	11.5	0.498	0.642	0.245	0.174
05	0.221	0.323	0.349	0.539	0.539	0.539	8.28	8.56	0.416	0.580	0.221	0.174
06	0.198	0.375	0.323	0.539	0.539	0.539	8.84	10.8	0.349	0.323	0.221	0.174
07	0.198	0.349	0.297	0.539	0.539	0.539	9.12	11.1	0.323	0.271	0.198	0.198
08	0.198	0.349	0.297	0.539	0.539	0.539	8.28	11.1	0.271	0.245	0.198	0.174
09	0.198	0.375	0.297	0.539	0.539	0.539	9.40	10.2	0.245	0.245	0.198	0.174
10	0.198	0.271	0.297	0.539	0.539	0.539	9.68	8.56	0.221	0.221	0.198	0.174
11	0.198	0.271	0.297	0.539	0.539	0.539	9.68	7.48	0.221	0.221	0.198	0.174
12	0.198	0.271	0.297	0.539	0.539	0.539	10.8	6.44	0.271	0.245	0.198	0.174
13	0.198	0.245	0.297	0.539	0.539	0.539	11.5	6.44	0.323	0.245	0.198	0.174
14	0.198	0.271	0.349	0.539	0.539	0.539	18.9	6.18	0.349	0.221	0.174	0.174
15	0.198	0.271	0.349	0.539	0.539	0.828	19.4	5.05	0.323	0.221	0.174	0.174
16	0.198	0.271	0.457	0.539	0.539	2.92	20.7	4.70	0.323	0.221	0.174	0.174
17	0.498	0.271	0.375	0.539	0.539	2.92	19.8	4.53	0.323	0.221	0.174	0.174
18	0.375	0.271	0.271	0.539	0.539	3.06	21.2	4.35	0.349	0.221	0.198	0.198
19	0.323	0.271	0.297	0.539	0.539	3.06	18.0	3.83	0.349	0.221	0.198	0.198
20	0.349	0.271	0.297	0.539	0.539	3.06	16.8	3.50	0.349	0.221	0.198	0.198
21	0.349	0.271	0.271	0.539	0.539	3.06	18.9	4.18	0.323	0.221	0.221	0.198
22	0.349	0.271	0.271	0.539	0.539	3.06	17.6	3.50	0.323	0.221	0.245	0.198
23	0.297	0.271	0.416	0.539	0.539	3.06	16.4	3.36	0.297	0.221	0.221	0.221
24	0.221	0.271	0.416	0.539	0.539	3.06	18.9	3.21	0.297	0.221	0.221	0.198
25	0.221	0.271	0.416	0.539	0.539	3.06	18.0	2.62	0.297	0.221	0.198	0.198
26	0.221	0.271	0.539	0.539	0.539	3.06	15.7	1.40	0.271	0.221	0.198	0.221
27	0.221	0.297	0.539	0.539	0.539	3.06	12.8	1.14	0.271	0.221	0.198	0.221
28	0.221	0.297	0.539	0.539	0.539	3.36	9.68	1.08	0.245	0.271	0.198	0.221
29	0.221	0.349	0.539	0.539	-----	3.65	9.12	1.01	0.271	0.271	0.198	0.221
30	0.221	0.323	0.539	0.539	-----	3.65	12.5	1.01	0.297	0.271	0.198	0.221
31	0.221	-----	0.539	0.539	-----	3.65	-----	1.01	-----	0.245	0.174	-----
Maks.	0.828	0.580	0.828	0.539	0.539	3.65	51.5	16.1	1.14	2.18	1.40	0.245
Min.	0.198	0.221	0.221	0.539	0.539	0.539	1.01	1.01	0.198	0.198	0.174	0.151
Ortalama	0.245	0.288	0.369	0.539	0.539	1.91	13.2	5.86	0.345	0.287	0.207	0.188
LT/SN/Km2	1.63	1.92	2.46	3.59	3.59	12.7	87.7	39.1	2.30	1.91	1.38	1.26
AKIM mm.	4.37	4.97	6.59	9.62	8.69	34.1	227.	105.	5.97	5.12	3.70	3.25
MİL. M3	0.656	0.745	0.988	1.44	1.30	5.11	34.1	15.7	0.895	0.768	0.555	0.488

SU YILI (2006) YILLIK TOPLAM AKIM 62.74 MİLYON M3 418 MM. 13.3 LT/SN/Km2

24. Aras Havzasi

D24A089 DİGOR S. DÜZGEÇİT

YERİ : **KARS - IĞDIR KARA YOLU GÜZERGAHINDA DİGOR İLÇESİ DÜZGEÇİT KÖYÜNDEDİR.**
43°35'2" Doğu - 40°16'56" Kuzey

YAĞIŞ ALANI : **605,00 km2** **YAKLAŞIK KOT : 1355 m**

GÖZLEM SÜRESİ : **01.10.1998 - 30.09.2006**

ORTALAMA AKIMLAR : **Gözlem süresinde 0.898 m3/sn. (4 Yıllık) 2006 Su yılında 0.898 m3/sn.**

ANLIK EN ÇOK VE EN AZ AKIMLAR:

2006 Su yılında anlık ençok akım	:	**23.3**	**m3/sn**	**01.04.2006**
2006 Su yılında anlık enaz akım	:	**0.055**	**m3/sn**	**28.09.2006**
Gözlem süresinde anlık ençok akım	:	**23.3**	**m3/sn**	**01.04.2006**
Gözlem süresinde anlık enaz akım	:	**0.006**	**m3/sn**	**17.12.1999**

Akımlar 01 Ekim 2005 'den 30 Eylül 2006' a kadar m3/sn olarak

Gün	Ekim	Kasım	Aralık	Ocak	Şubat	Mart	Nisan	Mayıs	Haziran	Temmuz	Ağustos	Eylül
01	0.380	0.460	0.321	0.232	0.232	0.232	15.6	3.10	0.380	1.29	0.350	0.350
02	0.350	0.460	0.291	0.232	0.232	0.232	12.4	5.13	0.380	0.840	0.321	0.262
03	0.321	0.420	0.291	0.232	0.232	0.232	14.5	2.74	0.420	0.912	0.291	0.291
04	0.380	0.380	0.291	0.232	0.232	0.291	8.45	12.0	0.380	3.52	0.321	0.262
05	0.500	0.420	0.321	0.232	0.232	0.380	2.20	3.10	0.321	1.06	0.321	0.262
06	0.380	0.460	0.321	0.232	0.232	0.291	2.09	2.92	0.321	0.788	0.380	0.232
07	0.321	0.500	0.291	0.232	0.232	0.350	1.76	6.36	0.321	0.632	0.500	0.321
08	0.321	0.500	0.291	0.232	0.232	0.420	1.65	3.73	0.321	0.580	0.500	0.350
09	0.321	0.460	0.232	0.232	0.232	0.500	2.56	2.56	0.321	0.540	0.460	0.380
10	0.321	0.350	0.232	0.232	0.232	0.632	3.31	2.09	0.291	0.540	0.420	0.500
11	0.321	0.321	0.232	0.232	0.232	0.580	3.31	1.76	0.232	0.540	0.420	0.540
12	0.321	0.321	0.232	0.232	0.232	0.580	2.74	1.56	0.232	0.500	0.420	0.540
13	0.321	0.321	0.232	0.232	0.232	0.580	2.38	1.38	0.262	0.500	0.350	0.540
14	0.321	0.321	0.232	0.232	0.232	0.684	2.20	1.38	0.321	0.500	0.380	0.540
15	0.291	0.321	0.232	0.232	0.232	0.840	1.98	1.29	0.321	0.500	0.500	0.632
16	0.321	0.321	0.232	0.232	0.232	0.736	2.09	1.20	0.291	0.500	0.460	0.632
17	0.321	0.321	0.232	0.232	0.232	0.840	2.20	1.65	0.321	0.460	0.460	0.632
18	0.420	0.321	0.232	0.232	0.232	0.788	1.87	1.56	0.291	0.460	0.460	0.580
19	0.321	0.321	0.232	0.232	0.232	0.736	1.47	1.38	0.291	0.460	0.500	0.580
20	0.350	0.321	0.232	0.232	0.232	0.632	1.20	1.29	0.262	0.460	0.500	0.540
21	0.380	0.321	0.232	0.232	0.232	0.540	1.98	1.13	0.232	0.420	0.460	0.500
22	0.350	0.350	0.232	0.232	0.232	0.580	2.92	1.13	0.262	0.420	0.500	0.540
23	0.321	0.350	0.232	0.232	0.232	0.632	2.09	1.13	0.232	0.420	0.632	0.580
24	0.321	0.262	0.232	0.232	0.232	0.984	5.87	0.788	0.210	0.420	0.788	0.540
25	0.321	0.350	0.232	0.232	0.232	1.98	5.13	0.736	0.188	0.420	0.580	0.540
26	0.321	0.350	0.232	0.232	0.232	3.52	3.31	0.632	0.232	0.420	0.540	0.500
27	0.321	0.321	0.232	0.232	0.232	3.73	1.98	0.540	0.291	0.420	0.460	0.500
28	0.321	0.291	0.232	0.232	0.232	3.52	1.76	0.540	0.350	0.420	0.460	0.500
29	0.500	0.291	0.232	0.232	-----	4.89	1.56	0.460	0.540	0.420	0.500	0.460
30	0.460	0.291	0.232	0.232	-----	5.13	1.98	0.420	0.840	0.420	0.460	0.460
31	0.460	-----	0.232	0.232	-----	9.56	-----	0.420	-----	0.420	0.540	-----
Maks.	0.580	0.788	0.840	0.232	0.232	12.8	23.3	14.1	1.56	5.13	1.38	1.06
Min.	0.232	0.166	0.232	0.232	0.232	0.110	1.20	0.380	0.188	0.420	0.147	0.055
Ortalama	0.354	0.360	0.250	0.232	0.232	1.47	3.82	2.13	0.322	0.652	0.459	0.470
LT/SN/Km2	0.585	0.595	0.413	0.383	0.383	2.43	6.31	3.52	0.532	1.08	0.759	0.776
AKIM mm.	1.57	1.54	1.11	1.03	0.928	6.52	16.4	9.44	1.38	2.89	2.03	2.01
MİL. M3	0.949	0.933	0.670	0.621	0.561	3.94	9.90	5.71	0.834	1.75	1.23	1.22

SU YILI (2006) YILLIK TOPLAM AKIM 28.32 MİLYON M3 47 MM. 1.5 LT/SN/Km2

24. Aras Havzasi

D24A090 KARAHAN Ç. TAŞDERE

YERİ : **KARS AKYAKA YOLUNDA CEBECİ KÖYÜNÜ GEÇTİKTEN SONRA TAŞDERE KÖYÜNE VARMADAN KÖPRÜNÜN 20 M MANSABINDADIR.**
43°35'21" Doğu - 40°51'40" Kuzey

YAĞIŞ ALANI : **76,00 km2** **YAKLAŞIK KOT : 1745 m**

GÖZLEM SÜRESİ : **01.10.1998 - 30.09.2006**

ORTALAMA AKIMLAR : **Gözlem süresinde 1.339 m3/sn. (6 Yıllık) 2006 Su yılında 1.608 m3/sn.**

ANLIK EN ÇOK VE EN AZ AKIMLAR:

2006 Su yılında anlık ençok akım	**:**	**13.2**	**m3/sn**	**11.04.2006**
2006 Su yılında anlık enaz akım	**:**	**0.084**	**m3/sn**	**20.07.2006**
Gözlem süresinde anlık ençok akım	**:**	**22.2**	**m3/sn**	**20.04.2005**
Gözlem süresinde anlık enaz akım	**:**	**0.052**	**m3/sn**	**14.12.2000**

Akımlar 01 Ekim 2005 'den 30 Eylül 2006' a kadar m3/sn olarak

Gün	Ekim	Kasım	Aralık	Ocak	Şubat	Mart	Nisan	Mayıs	Haziran	Temmuz	Ağustos	Eylül
01	0.711	1.33	0.711	0.711	0.711	0.711	5.38	5.03	1.54	0.857	0.711	0.565
02	0.711	1.25	0.711	0.711	0.711	0.711	7.19	9.70	1.54	0.784	0.711	0.565
03	0.711	1.09	0.711	0.711	0.711	0.711	8.65	6.58	1.54	1.25	0.711	0.565
04	0.711	1.01	0.711	0.711	0.711	0.711	5.38	7.60	1.54	1.33	0.784	0.565
05	0.711	1.09	0.711	0.711	0.711	0.711	5.55	5.20	1.54	1.09	0.711	0.565
06	0.638	1.43	0.711	0.711	0.711	1.01	6.37	6.78	1.33	0.857	0.711	0.565
07	0.638	1.33	0.711	0.711	0.711	1.01	7.19	8.44	1.33	0.784	0.638	0.565
08	0.638	1.17	0.711	0.711	0.711	1.01	8.44	6.37	1.33	0.930	0.638	0.565
09	0.638	1.17	0.711	0.711	0.711	1.01	10.4	8.23	1.09	1.01	0.638	0.565
10	0.638	0.930	0.711	0.711	0.711	1.09	11.3	5.96	1.09	0.711	0.638	0.565
11	0.638	0.930	0.711	0.711	0.711	1.09	10.9	4.68	1.01	1.64	0.638	0.638
12	0.638	1.01	0.711	0.711	0.711	1.09	9.07	4.33	0.930	0.930	0.638	0.711
13	0.638	0.930	0.711	0.711	0.711	1.01	8.65	3.98	0.930	0.784	0.638	0.638
14	0.638	0.857	0.711	0.711	0.711	1.09	7.60	3.80	0.857	0.711	0.565	0.638
15	0.638	0.857	0.711	0.711	0.711	1.17	8.02	3.38	0.857	0.711	0.565	0.638
16	0.638	0.784	0.711	0.711	0.711	1.17	6.37	2.96	0.784	0.784	0.565	0.638
17	0.930	0.784	0.711	0.711	0.711	1.17	6.37	3.24	0.784	0.711	0.565	0.565
18	1.09	0.784	0.711	0.711	0.711	1.17	5.20	3.52	0.784	0.638	0.565	0.565
19	0.857	0.784	0.711	0.711	0.711	1.17	5.20	3.10	0.784	0.638	0.638	0.565
20	1.75	0.784	0.711	0.711	0.711	1.17	6.58	2.96	0.711	0.638	0.638	0.565
21	1.25	0.784	0.711	0.711	0.711	1.09	5.38	2.96	0.711	0.638	0.711	0.565
22	0.930	0.857	0.711	0.711	0.711	0.469	6.17	2.96	0.711	0.784	0.711	0.565
23	0.857	0.711	0.711	0.711	0.711	0.469	11.5	2.68	0.711	0.784	0.638	0.565
24	0.784	0.711	0.711	0.711	0.711	0.517	9.70	2.40	0.784	0.711	0.638	0.565
25	0.784	0.711	0.711	0.711	0.711	0.784	5.76	2.29	0.711	0.711	0.638	0.565
26	0.784	0.711	0.711	0.711	0.711	1.43	4.68	2.18	0.638	0.711	0.638	0.711
27	0.711	0.711	0.711	0.711	0.711	1.43	3.98	2.07	0.784	0.711	0.638	0.857
28	0.469	0.711	0.711	0.711	0.711	1.64	3.24	2.18	1.01	0.711	0.638	0.638
29	0.565	0.711	0.711	0.711	-----	1.85	5.38	1.96	0.930	0.711	0.565	0.638
30	0.857	0.711	0.711	0.711	-----	2.18	5.38	1.75	1.01	0.711	0.565	0.711
31	1.33	-----	0.711	0.711	-----	3.10	-----	1.64	-----	0.711	0.565	-----
Maks.	1.75	1.54	0.711	0.711	0.711	4.15	13.2	11.3	2.07	12.2	0.784	0.857
Min.	0.469	0.711	0.711	0.711	0.711	0.469	2.82	1.54	0.638	0.084	0.292	0.517
Ortalama	0.791	0.921	0.711	0.711	0.711	1.13	7.03	4.22	1.01	0.828	0.640	0.606
LT/SN/Km2	10.4	12.1	9.36	9.36	9.36	14.8	92.5	55.6	13.3	10.9	8.43	7.98
AKIM mm.	27.9	31.4	25.1	25.1	22.6	39.7	240.	149.	34.4	29.2	22.6	20.7
MİL. M3	2.12	2.39	1.90	1.90	1.72	3.02	18.2	11.3	2.62	2.22	1.72	1.57

SU YILI (2006) YILLIK TOPLAM AKIM 50.68 MİLYON M3 667 MM. 21.2 LT/SN/Km2

24. Aras Havzasi

D24A091 KARS Ç. FAKÜLTE ÖNÜ

YERİ : **KARS DEREİÇİ YOLU ÜZERİNDE FEN FAKÜLTESİ ÖNÜNDEDİR.**
43°5'38" Doğu - 40°37'0" Kuzey

YAĞIŞ ALANI : **2510,00 km2** **YAKLAŞIK KOT : 1690 m**

GÖZLEM SÜRESİ : **01.10.1998 - 30.09.2006**

ORTALAMA AKIMLAR : **Gözlem süresinde 11.225 m3/sn. (3 Yıllık) 2006 Su yılında 11.225 m3/sn.**

ANLIK EN ÇOK VE EN AZ AKIMLAR:

2006 Su yılında anlık ençok akım	:	**66.5**	**m3/sn**	**26.04.2006**
2006 Su yılında anlık enaz akım	:	**1.07**	**m3/sn**	**18.09.2006**
Gözlem süresinde anlık ençok akım	:	**72.0**	**m3/sn**	**11.05.2000**
Gözlem süresinde anlık enaz akım	:	**0.410**	**m3/sn**	**14.07.2000**

Akımlar 01 Ekim 2005 'den 30 Eylül 2006' a kadar m3/sn olarak

Gün	Ekim	Kasım	Aralık	Ocak	Şubat	Mart	Nisan	Mayıs	Haziran	Temmuz	Ağustos	Eylül
01	6.49	15.5	8.53	6.96	6.96	6.96	48.8	41.7	11.7	11.4	2.36	1.95
02	5.37	15.8	7.42	6.96	6.96	6.96	53.9	46.6	11.1	12.0	2.36	1.95
03	4.73	12.0	7.70	6.96	6.96	6.96	52.2	36.9	14.5	17.2	2.69	1.95
04	5.37	10.2	8.25	6.96	6.96	6.96	53.9	43.3	12.0	13.9	2.53	1.95
05	6.04	9.64	7.98	6.96	6.96	6.96	41.1	36.0	10.8	10.8	2.36	1.95
06	5.82	11.1	7.70	6.96	6.96	6.96	36.9	35.0	9.64	13.2	2.36	1.81
07	5.37	12.6	7.19	6.96	6.96	6.96	30.8	36.5	11.4	9.64	2.22	1.81
08	5.37	11.7	6.96	6.96	6.96	6.96	26.8	36.9	9.37	7.19	2.22	1.81
09	5.15	10.2	6.96	6.96	6.96	6.96	39.5	40.1	8.25	6.72	2.22	1.81
10	5.15	9.09	6.96	6.96	6.96	6.96	47.2	36.0	6.96	5.59	2.22	1.81
11	5.15	8.25	6.96	6.96	6.96	9.09	43.9	31.7	6.04	4.94	2.08	1.81
12	5.15	7.42	6.96	6.96	6.96	8.81	41.7	29.4	5.37	4.73	2.08	1.81
13	5.15	7.98	6.26	6.96	6.96	9.09	36.9	28.1	4.94	4.53	2.08	1.81
14	4.94	7.70	5.82	6.96	6.96	9.64	36.0	27.6	4.73	3.56	2.36	1.81
15	5.37	7.70	6.04	6.96	6.96	12.6	36.5	33.6	4.32	2.86	2.36	1.81
16	5.37	7.19	6.49	6.96	6.96	12.0	38.4	25.9	3.93	3.19	2.08	2.22
17	6.49	7.19	6.72	6.96	6.96	10.8	41.7	24.2	3.74	2.69	2.53	2.08
18	12.0	6.96	6.49	6.96	6.96	11.7	37.9	24.2	3.37	2.69	3.02	1.95
19	7.42	6.96	6.96	6.96	6.96	10.8	33.1	23.4	3.19	3.02	3.56	1.95
20	7.19	7.19	6.96	6.96	6.96	8.81	30.3	21.4	3.19	2.86	2.86	1.95
21	7.70	7.19	7.19	6.96	6.96	6.49	33.6	27.6	3.74	2.69	2.08	2.08
22	6.72	7.98	6.96	6.96	6.96	7.70	41.1	22.6	3.74	2.69	2.36	1.95
23	6.04	7.42	6.96	6.96	6.96	9.92	36.5	19.5	3.37	2.86	2.22	1.95
24	5.82	6.72	8.53	6.96	6.96	13.5	47.2	18.0	6.72	2.69	3.02	1.95
25	5.82	5.82	9.37	6.96	6.96	22.6	58.1	16.9	4.32	2.53	2.08	1.95
26	5.82	7.19	7.98	6.96	6.96	28.1	65.3	16.2	3.37	2.53	2.08	2.69
27	5.59	7.42	6.96	6.96	6.96	25.9	48.8	15.2	3.37	2.53	2.08	2.69
28	5.82	7.42	6.96	6.96	6.96	24.6	40.1	15.2	4.94	2.36	2.08	2.36
29	7.19	7.70	6.96	6.96	-----	27.6	32.2	13.9	11.4	2.36	2.08	2.22
30	8.53	7.98	6.96	6.96	-----	28.1	38.4	12.9	6.72	2.69	2.08	2.22
31	10.2	-----	6.96	6.96	-----	34.5	-----	12.3	-----	2.53	1.95	-----
Maks.	14.5	18.7	10.2	6.96	6.96	39.5	66.5	50.5	17.6	20.2	4.94	3.37
Min.	4.32	4.11	4.73	6.96	6.96	5.59	23.4	12.0	3.02	2.36	1.95	1.07
Ortalama	6.27	8.84	7.20	6.96	6.96	13.0	41.6	27.4	6.67	5.52	2.34	2.00
LT/SN/Km2	2.50	3.52	2.87	2.77	2.77	5.17	16.6	10.9	2.66	2.20	0.934	0.798
AKIM mm.	6.69	9.13	7.68	7.43	6.71	13.8	43.0	29.2	6.89	5.89	2.50	2.07
MİL. M3	16.8	22.9	19.3	18.6	16.8	34.7	108.	73.3	17.3	14.8	6.28	5.19

SU YILI (2006) YILLIK TOPLAM AKIM 353.97 MİLYON M3 141 MM. 4.5 LT/SN/Km2

24. Aras Havzasi

D24A092 SOĞUKSU D. KARATAŞLAR

YERİ : **YENİ ERZURUM KARAYAZI YOLUNUN 70 KM SİNDE ESKİ YOL ÜZERİNDEKİ KÖPRÜNÜN MANSABINDADIR**

41°58'50" Doğu - 39°50'2" Kuzey

YAĞIŞ ALANI : **165,00 km2** **YAKLAŞIK KOT : 1787 m**

GÖZLEM SÜRESİ : **01.10.1999 - 30.09.2006**

ORTALAMA AKIMLAR : **Gözlem süresinde 2.274 m3/sn. (5 Yıllık) 2006 Su yılında 2.211 m3/sn.**

ANLIK EN ÇOK VE EN AZ AKIMLAR:

2006 Su yılında anlık ençok akım	**:**	**25.4**	**m3/sn**	**16.04.2006**
2006 Su yılında anlık enaz akım	**:**	**0.420**	**m3/sn**	**25.09.2006**
Gözlem süresinde anlık ençok akım	**:**	**34.2**	**m3/sn**	**24.03.2001**
Gözlem süresinde anlık enaz akım	**:**	**0.390**	**m3/sn**	**20.06.2000**

İstasyon için kullanılmış anahtar bulunamadı.

Akımlar 01 Ekim 2005 'den 30 Eylül 2006' a kadar m3/sn olarak

Gün	Ekim	Kasım	Aralık	Ocak	Şubat	Mart	Nisan	Mayıs	Haziran	Temmuz	Ağustos	Eylül
01	0.780	1.55	0.780	1.03	1.15	0.685	3.32	13.1	1.31	1.70	1.03	0.780
02	0.780	1.15	0.780	1.15	1.15	0.780	3.54	11.9	1.15	1.55	1.15	0.780
03	0.685	1.15	0.780	1.15	1.15	0.780	4.46	13.8	1.31	2.00	1.15	0.685
04	0.780	1.15	0.904	1.15	1.15	0.780	4.20	11.9	2.34	2.00	1.03	0.780
05	0.685	1.15	0.904	1.15	1.15	0.780	4.46	8.49	2.15	1.70	0.904	0.780
06	0.685	1.15	0.904	1.15	1.15	0.780	3.98	11.5	2.00	1.55	0.904	1.28
07	0.685	1.15	0.904	1.15	1.15	0.780	3.76	10.8	2.00	1.40	0.904	0.904
08	0.685	1.03	0.780	1.15	1.15	0.780	4.20	11.2	1.70	1.28	0.780	0.904
09	0.685	0.780	0.780	1.15	0.780	0.780	6.50	9.48	1.55	1.15	0.780	0.904
10	0.590	0.780	0.780	1.15	0.590	0.685	8.89	8.18	1.55	1.15	0.780	0.904
11	0.685	0.780	0.780	1.15	1.15	0.780	10.7	6.63	1.40	1.03	0.780	0.904
12	0.590	0.685	0.780	1.15	0.780	0.904	12.5	6.63	1.28	0.904	0.780	0.904
13	0.590	0.685	0.685	1.15	1.15	0.904	13.5	6.63	1.28	0.904	0.780	1.03
14	0.590	0.685	0.780	1.15	0.510	0.904	14.5	6.32	1.28	0.904	0.780	1.03
15	0.590	0.685	0.780	1.15	0.425	1.03	15.9	6.32	1.15	0.904	0.685	1.03
16	0.685	0.685	0.685	1.15	0.510	0.904	18.5	5.40	1.15	0.904	0.685	1.03
17	2.53	0.685	0.685	1.15	0.590	0.904	15.9	4.50	1.15	0.904	0.780	1.03
18	1.15	0.685	0.590	1.15	0.685	0.904	16.7	4.20	1.03	0.904	0.780	1.03
19	1.15	0.685	0.590	1.15	0.685	0.904	12.8	3.96	1.03	0.904	0.904	1.03
20	1.15	0.685	0.685	1.15	0.685	0.904	12.5	3.72	0.904	0.904	0.904	1.03
21	1.03	0.780	0.590	1.15	0.685	0.780	17.6	4.50	0.904	0.904	0.904	1.03
22	1.03	0.685	0.590	1.15	0.685	0.904	13.8	3.96	0.904	0.904	0.904	1.03
23	1.03	0.510	0.685	1.15	0.685	0.904	12.8	3.48	0.904	0.780	0.904	0.560
24	1.03	0.685	0.590	1.15	0.685	1.03	18.5	3.24	0.904	0.780	0.904	0.485
25	1.03	0.780	0.590	1.15	0.685	1.55	17.1	2.79	0.780	0.904	0.780	0.420
26	1.03	0.685	0.685	1.15	0.685	1.70	12.2	2.58	0.904	0.904	0.904	0.485
27	1.03	0.685	0.590	1.15	0.780	1.55	10.7	2.16	0.904	0.904	0.904	0.485
28	1.03	0.685	0.685	1.15	0.590	1.70	8.58	1.79	1.28	0.904	0.904	0.420
29	1.15	0.780	0.780	1.15	-----	1.85	7.67	1.63	1.28	1.28	0.904	0.420
30	1.70	0.780	0.904	1.15	-----	2.00	8.89	1.47	1.15	1.15	0.780	0.420
31	2.00	-----	1.03	1.15	-----	2.53	-----	1.31	-----	1.03	0.780	-----
Maks.	4.98	2.15	1.40	1.15	1.15	3.54	25.4	21.4	3.10	3.32	1.85	1.28
Min.	0.590	0.425	0.425	1.03	0.425	0.510	2.53	1.31	0.780	0.685	0.685	0.420
Ortalama	0.963	0.835	0.744	1.15	0.829	1.07	10.6	6.24	1.29	1.13	0.866	0.817
LT/SN/Km2	5.83	5.06	4.51	6.95	5.03	6.48	64.4	37.8	7.80	6.86	5.25	4.95
AKIM mm.	15.6	13.1	12.1	18.6	12.2	17.4	167.	101.	20.2	18.4	14.1	12.8
MİL. M3	2.58	2.16	1.99	3.07	2.01	2.86	27.5	16.7	3.34	3.03	2.32	2.12

SU YILI (2006) YILLIK TOPLAM AKIM 69.68 MİLYON M3 422 MM. 13.4 LT/SN/Km2

24. Aras Havzasi

D24A094 ALABALIK D. KOÇKÖYÜ

YERİ : **ARPAÇAY KOÇKÖYÜ GİRIŞINDE 200 M MENBADADIR.**
43°31'22" Doğu - 40°52'3" Kuzey

YAĞIŞ ALANI : **73,00 km2** **YAKLAŞIK KOT : 1794 m**

GÖZLEM SÜRESİ : **01.10.2000 - 30.09.2006**

ORTALAMA AKIMLAR : **Gözlem süresinde 0.988 m3/sn. (5 Yıllık) 2006 Su yılında 1.051 m3/sn.**

ANLIK EN ÇOK VE EN AZ AKIMLAR:

2006 Su yılında anlık ençok akım	:	**10.3**	**m3/sn**	**24.04.2006**
2006 Su yılında anlık enaz akım	:	**0.007**	**m3/sn**	**03.09.2006**
Gözlem süresinde anlık ençok akım	:	**11.2**	**m3/sn**	**20.04.2005**
Gözlem süresinde anlık enaz akım	:	**0.007**	**m3/sn**	**03.09.2006**

Akımlar 01 Ekim 2005 'den 30 Eylül 2006' a kadar m3/sn olarak

Gün	Ekim	Kasım	Aralık	Ocak	Şubat	Mart	Nisan	Mayıs	Haziran	Temmuz	Ağustos	Eylül
01	0.270	0.270	0.146	0.172	0.172	0.172	5.27	4.93	1.06	0.203	0.146	0.099
02	0.316	0.815	0.146	0.172	0.172	0.172	5.95	7.43	0.896	0.203	0.146	0.099
03	0.563	0.752	0.146	0.172	0.172	0.172	6.69	5.78	0.896	0.362	0.172	0.099
04	0.408	0.500	0.121	0.172	0.172	0.172	5.27	6.88	0.815	0.454	0.146	0.099
05	0.235	0.454	0.121	0.172	0.172	0.172	3.57	5.44	0.815	0.362	0.146	0.099
06	0.172	0.408	0.121	0.172	0.172	0.146	2.62	7.62	0.689	0.316	0.121	0.099
07	0.146	0.362	0.121	0.172	0.172	0.172	3.29	8.37	0.626	0.270	0.121	0.121
08	0.121	0.235	0.121	0.172	0.172	0.172	3.84	7.25	0.563	0.270	0.121	0.099
09	0.121	0.270	0.121	0.172	0.172	0.172	6.14	7.99	0.454	0.316	0.121	0.099
10	0.121	0.270	0.121	0.172	0.172	0.172	8.56	6.69	0.408	0.235	0.099	0.099
11	0.146	0.270	0.121	0.172	0.172	0.172	8.18	5.61	0.316	0.454	0.099	0.099
12	0.146	0.235	0.121	0.172	0.172	0.172	7.80	5.27	0.316	0.270	0.099	0.146
13	0.172	0.270	0.121	0.172	0.172	0.203	7.25	5.10	0.270	0.203	0.099	0.146
14	0.172	0.235	0.121	0.172	0.172	0.235	7.25	4.93	0.270	0.203	0.099	0.146
15	0.235	0.235	0.121	0.172	0.172	0.316	7.25	4.11	0.270	0.203	0.099	0.146
16	0.563	0.203	0.121	0.172	0.172	0.316	7.06	3.98	0.235	0.203	0.099	0.146
17	0.408	0.203	0.121	0.172	0.172	0.316	7.62	4.25	0.203	0.172	0.099	0.146
18	0.270	0.146	0.121	0.172	0.172	0.270	6.32	2.88	0.203	0.203	0.099	0.146
19	0.235	0.172	0.121	0.172	0.172	0.270	5.95	2.62	0.203	0.172	0.099	0.121
20	0.203	0.203	0.121	0.172	0.172	0.235	5.44	2.35	0.203	0.172	0.099	0.146
21	0.500	0.235	0.121	0.172	0.172	0.235	5.44	2.62	0.203	0.172	0.121	0.172
22	0.316	0.172	0.121	0.172	0.172	0.235	6.32	2.48	0.172	0.172	0.146	0.172
23	0.235	0.172	0.121	0.172	0.172	0.316	5.10	2.22	0.172	0.172	0.121	0.172
24	0.203	0.172	0.121	0.172	0.172	0.563	5.44	2.01	0.172	0.172	0.099	0.172
25	0.203	0.172	0.121	0.172	0.172	0.977	8.94	2.01	0.146	0.172	0.121	0.203
26	0.203	0.172	0.121	0.172	0.172	1.41	8.75	1.70	0.146	0.172	0.146	0.203
27	0.203	0.203	0.121	0.172	0.172	1.32	5.78	1.60	0.203	0.172	0.121	0.172
28	0.203	0.172	0.121	0.172	0.172	1.14	4.42	1.60	0.203	0.172	0.121	0.172
29	0.203	0.172	0.121	0.172	-----	1.60	3.70	1.32	0.316	0.172	0.099	0.172
30	0.454	0.172	0.121	0.172	-----	2.88	3.29	1.14	0.316	0.146	0.099	0.172
31	0.362	-----	0.121	0.172	-----	3.84	-----	1.06	-----	0.146	0.099	-----
Maks.	0.563	1.60	0.146	0.172	0.172	5.44	10.3	9.51	1.22	0.896	1.14	0.235
Min.	0.121	0.099	0.121	0.172	0.172	0.121	2.48	0.896	0.121	0.146	0.036	0.007
Ortalama	0.262	0.277	0.123	0.172	0.172	0.604	5.95	4.17	0.392	0.229	0.117	0.139
LT/SN/Km2	3.58	3.80	1.69	2.36	2.36	8.27	81.5	57.1	5.37	3.13	1.60	1.91
AKIM mm.	9.60	9.85	4.53	6.31	5.70	22.2	211.	153.	13.9	8.39	4.29	4.95
MİL. M3	0.701	0.719	0.331	0.461	0.416	1.62	15.4	11.2	1.02	0.612	0.313	0.361

SU YILI (2006) YILLIK TOPLAM AKIM 33.15 MİLYON M3 454 MM. 14.4 LT/SN/Km2

25
VAN GÖLÜ KAPALI HAVZASI

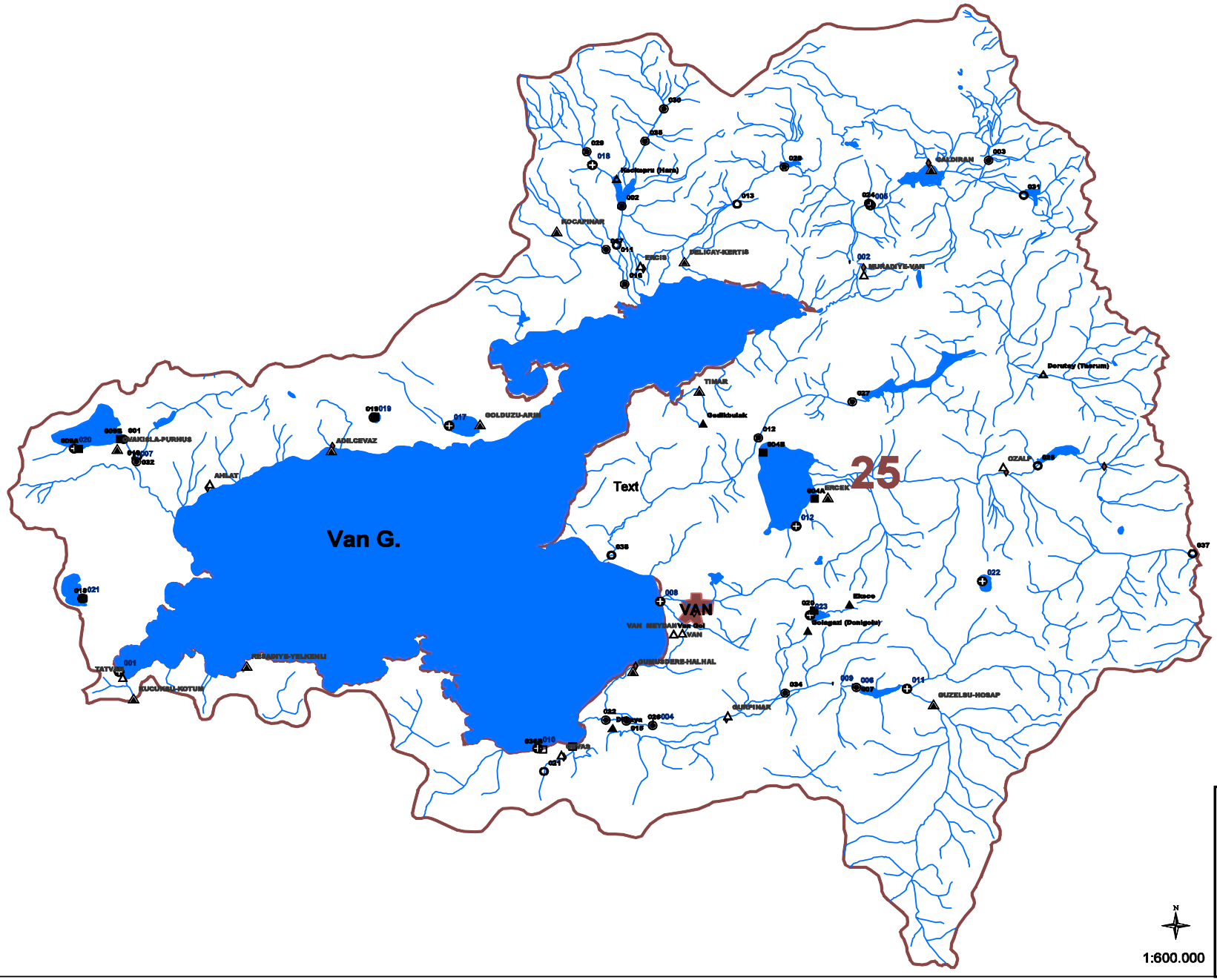
Van G.
VAN
25
Text
KOCAPINAR
ERCIS
MURADIYE-VAN
TIMAR
GOLDUZU-ARIN
ADILCEVAZ
AHLAT
OZALP
ERCEK
GUZELSU-HOSAP
GUNPINAR
TATVAN
1:600.000
N
25.VANKAPALI HAVZASI
DSI-AGI(Acik)
DSI-AGI(Kapali)
DSI-GGI(Acik)
DSI-GGI(Kapali)
EIE-AGI(Acik)
EIE-AGI(Kapali)
DSI-MGI(Acik)
DSI-MGI(Kapali)
DMI-MGI(Acik)
DMI-MGI(Kapali)

25. Van Gölü Havzasi

D25A013 DELİÇAY PAYKÖY

YERİ : ERCİŞE 22 KM MESAFEDE KERTİS-KIZILÖREN YOLUNUN 8 KM SİNDEDİR.
43°32'0" Doğu - 39°6'0" Kuzey

YAĞIŞ ALANI : 329,40 km2 **YAKLAŞIK KOT** : 1992 m

GÖZLEM SÜRESİ : 01.10.1964 - 30.09.2006

ORTALAMA AKIMLAR : Gözlem süresinde 5.161 m3/sn. (32 Yıllık) 2006 Su yılında 4.415 m3/sn.

ANLIK EN ÇOK VE EN AZ AKIMLAR:

2006 Su yılında anlık ençok akım	:	24.7	m3/sn	09.05.2006
2006 Su yılında anlık enaz akım	:	1.72	m3/sn	01.11.2005
Gözlem süresinde anlık ençok akım	:	72.4	m3/sn	16.04.1998
Gözlem süresinde anlık enaz akım	:	0.026	m3/sn	19.09.2000

8. Anahtar Eğrisi (Seviyeler cm olarak)

Seviye	Akım	Seviye	Akım	Seviye	Akım	Seviye	Akım
20	0.012	70	10.0	120	27.5	170	47.0
30	0.620	80	13.5	130	31.0	180	51.0
40	1.8	90	17.0	140	35.0	190	55.0
50	3.6	100	20.5	150	39.0	200	59.0
60	6.2	110	24.0	160	43.0	250	83.0

Akımlar 01 Ekim 2005 'den 30 Eylül 2006' a kadar m3/sn olarak

Gün	Ekim	Kasım	Aralık	Ocak	Şubat	Mart	Nisan	Mayıs	Haziran	Temmuz	Ağustos	Eylül
01	2.40	1.72	1.72	1.72	1.72	1.72	6.32	19.8	4.88	4.20	2.13	2.13
02	2.40	1.72	1.72	1.72	1.72	1.72	6.56	18.8	4.88	4.40	2.13	2.13
03	2.40	1.72	1.72	1.72	1.72	1.72	7.44	17.7	4.88	4.40	2.13	2.13
04	2.40	1.72	1.72	1.72	1.72	1.72	8.40	20.5	4.88	4.40	2.13	2.13
05	2.40	1.72	1.72	1.72	1.72	1.72	8.72	22.3	4.88	4.40	2.13	2.13
06	2.40	1.72	1.72	1.72	1.72	1.72	8.72	22.3	4.88	4.00	2.13	1.99
07	2.40	1.72	1.72	1.72	1.72	1.72	9.36	22.6	4.88	4.00	2.13	1.99
08	2.40	1.72	1.72	1.72	1.72	1.72	9.36	23.3	4.88	3.80	2.13	1.99
09	2.40	1.72	1.72	1.72	1.72	1.72	11.1	22.6	4.88	3.80	2.13	1.99
10	2.40	1.72	1.72	1.72	1.72	1.72	11.1	19.8	4.88	3.40	2.13	1.99
11	2.40	1.72	1.72	1.72	1.72	1.72	11.8	17.0	4.88	3.40	2.13	1.99
12	2.40	1.72	1.72	1.72	1.72	1.72	11.8	15.6	4.88	3.00	2.13	1.99
13	2.40	1.72	1.72	1.72	1.72	1.72	12.8	14.6	4.88	3.00	2.13	1.99
14	2.40	1.72	1.72	1.72	1.72	1.72	14.2	14.2	4.88	3.00	2.13	1.99
15	2.40	1.72	1.72	1.72	1.72	1.72	14.6	13.2	4.88	2.60	2.13	1.99
16	2.40	1.72	1.72	1.72	1.72	1.99	14.9	12.8	4.88	2.60	2.13	1.99
17	2.40	1.72	1.72	1.72	1.72	2.26	15.6	13.9	4.88	2.40	2.13	1.99
18	2.40	1.72	1.72	1.72	1.72	2.26	15.6	13.5	4.88	2.40	2.13	1.99
19	2.40	1.72	1.72	1.72	1.72	2.26	16.3	13.5	4.88	2.40	2.13	1.99
20	2.40	1.72	1.72	1.72	1.72	2.26	16.3	13.5	4.88	2.40	2.13	1.99
21	2.40	1.72	1.72	1.72	1.72	2.26	15.6	13.5	4.88	2.40	2.13	1.99
22	2.40	1.72	1.72	1.72	1.72	2.26	16.0	17.4	4.88	2.40	2.13	1.99
23	2.40	1.72	1.72	1.72	1.72	2.40	16.3	12.8	4.88	2.40	2.13	1.99
24	2.40	1.72	1.72	1.72	1.72	3.60	16.3	11.4	4.88	2.40	2.13	1.99
25	2.40	1.72	1.72	1.72	1.72	3.80	18.4	10.7	4.88	2.40	2.13	1.99
26	2.40	1.72	1.72	1.72	1.72	3.80	18.8	10.4	4.88	2.40	2.13	1.99
27	2.40	1.72	1.72	1.72	1.72	3.80	18.8	10.4	4.20	2.40	2.13	1.99
28	2.40	1.72	1.72	1.72	1.72	4.20	19.8	10.4	4.20	2.13	2.13	1.99
29	2.40	1.72	1.72	1.72	-----	4.20	19.8	11.1	4.20	2.13	2.13	1.99
30	2.40	1.72	1.72	1.72	-----	4.20	19.8	11.1	4.00	2.13	2.13	2.13
31	2.40	-----	1.72	1.72	-----	5.12	-----	9.68	-----	2.13	2.13	-----
Maks.	2.40	1.72	1.72	1.72	1.72	6.08	19.8	24.7	5.36	4.40	2.13	2.13
Min.	2.40	1.72	1.72	1.72	1.72	1.72	6.08	9.68	4.00	2.13	2.13	1.99
Ortalama	2.40	1.72	1.72	1.72	1.72	2.47	13.7	15.5	4.78	3.01	2.13	2.02
LT/SN/Km2	7.29	5.22	5.22	5.22	5.22	7.49	41.5	47.0	14.5	9.14	6.47	6.13
AKIM mm.	19.5	13.5	14.0	14.0	12.6	20.1	108.	126.	37.6	24.5	17.3	15.9
MİL. M3	6.43	4.46	4.61	4.61	4.16	6.61	35.5	41.5	12.4	8.06	5.70	5.23

SU YILI (2006) YILLIK TOPLAM AKIM 139.27 MİLYON M3 423 MM. 13.4 LT/SN/Km2

BÖLÜM II
GÖL RASAT İSTASYONLARI

8 - BATI AKDENIZ HAVZASI

08006 - KARAGÖL-GÖLRASATI

YERİ :(29° 49' 0" D - 36° 43' 0" K) ELMALI İLÇESİ YUVA KÖYÜ YOLUNUN 14.5 KM SİNDEDİR.

YAĞIŞ ALANI : 500.8 Km2 YAKLAŞIK KOT : 1027 m.

GÖZLEM SÜRESİ :25/05/1958 - 30/09/2006

EN YÜKSEK VE EN DÜŞÜK SEVİYELER:

2006 Su yılında en yüksek seviye	:	295	cm.	04/05/2006
2006 Su yılında en düşük seviye	:	163	cm.	29/09/2006
Gözlem süresinde en yüksek seviye	:	368	cm.	08/05/1970
Gözlem süresinde en düşük seviye	:	0	cm.	01/11/1971

GÖZLEM SÜRESİNDE ORTALAMA SEVİYE : 99.85 cm.

SEVİYELER 1 EKİM 1905 'DEN 30 EYLÜL 2006 'A KADAR CM. OLARAK

GUN/AY	EKİM	KASIM	ARALIK	OCAK	ŞUBAT	MART	NİSAN	MAYIS	HAZİRAN	TEMMUZ	AĞUSTOS	EYLÜL
1	197	207	213	216	222	227	283	294	287	209	183	170
2	197	208	213	216	222	227	283	294	287	207	182	169
3	197	208	213	217	223	227	284	294	286	205	181	169
4	198	208	213	217	223	227	285	295	285	203	180	169
5	198	208	213	217	223	228	286	295	285	202	179	168
6	199	208	213	217	223	228	287	295	284	202	178	168
7	200	209	214	217	223	228	288	295	283	201	177	168
8	200	209	214	218	223	228	288	295	282	201	177	168
9	201	209	214	218	223	228	288	295	281	201	176	167
10	201	209	214	218	223	228	289	295	280	200	176	167
11	201	210	214	218	224	229	289	295	279	200	175	167
12	202	210	214	218	224	229	290	294	278	200	175	167
13	202	210	214	219	224	229	290	294	277	200	174	167
14	202	210	214	219	224	230	290	294	276	199	174	166
15	203	210	214	219	224	230	290	294	275	199	174	166
16	203	210	214	219	224	233	291	294	274	198	173	166
17	203	211	214	220	224	235	291	293	265	198	173	166
18	204	211	214	220	224	238	291	293	260	197	173	166
19	204	211	214	220	225	241	292	293	254	196	172	166
20	204	212	214	220	225	244	292	292	248	195	172	166
21	205	212	215	220	225	246	292	292	243	194	172	165
22	205	212	215	221	225	248	293	292	237	193	171	165
23	205	212	215	221	225	252	293	292	233	192	171	165
24	206	212	215	221	225	256	293	291	229	191	171	165
25	206	213	215	221	226	260	293	291	225	190	171	164
26	206	213	215	221	226	265	293	290	221	189	170	164
27	206	213	215	222	226	270	294	290	217	188	170	164
28	207	213	215	222	226	274	294	290	215	187	170	164
29	207	213	216	222	---	277	294	289	213	186	170	163
30	207	213	216	222	---	279	294	289	211	185	170	163
31	207	---	216	222	---	281	---	288	---	184	170	---
MAKS.	207	213	216	222	226	282	294	295	287	209	183	170
MIN.	197	207	213	216	222	227	283	288	210	184	170	163
ORTALAMA	202	210	214	219	224	242	290	292	259	196	174	166

YILLIK ORT.:225 cm.

8 - BATI AKDENIZ HAVZASI

08063 - ALAKIR BARAJI-GÖLRASATI

YERİ :(30° 14' 0" D - 36° 26' 0" K) Finike-kumluca yolunun 16.km sindeki hıdırkaya köyünden sola ayrılan yolun 8 km.sindeki baraj gölündedir.

YAĞIŞ ALANI : 634 Km2 YAKLAŞIK KOT : 103 m.

GÖZLEM SÜRESİ :01/01/1970 - 30/09/2006

EN YÜKSEK VE EN DÜŞÜK SEVİYELER:

2006 Su yılında en yüksek seviye	:	2256	cm.	14/03/2006
2006 Su yılında en düşük seviye	:	1055	cm.	30/09/2006
Gözlem süresinde en yüksek seviye	:	2605	cm.	09/02/1996
Gözlem süresinde en düşük seviye	:	200	cm.	22/08/1970

GÖZLEM SÜRESİNDE ORTALAMA SEVİYE : 1568 cm.

SEVİYELER 1 EKİM 1905 'DEN 30 EYLÜL 2006 'A KADAR CM. OLARAK

GUN/AY	EKİM	KASIM	ARALIK	OCAK	ŞUBAT	MART	NİSAN	MAYIS	HAZİRAN	TEMMUZ	AĞUSTOS	EYLÜL
1	1517	1437	1455	1564	1958	2160	2171	2156	2022	1746	1448	1198
2	1516	1433	1451	1568	1962	2159	2171	2154	2012	1736	1440	1194
3	1516	1431	1447	1575	1968	2158	2170	2153	2002	1728	1432	1190
4	1515	1428	1444	1578	1970	2158	2169	2152	1992	1720	1423	1186
5	1512	1426	1444	1582	1974	2158	2168	2152	1986	1712	1415	1182
6	1509	1424	1441	1586	1978	2158	2168	2152	1977	1704	1407	1178
7	1516	1421	1438	1586	2008	2158	2167	2151	1968	1696	1398	1174
8	1504	1419	1435	1586	2052	2158	2167	2148	1958	1687	1390	1168
9	1502	1418	1433	1590	2120	2160	2166	2146	1950	1678	1382	1160
10	1500	1418	1429	1598	2146	2160	2166	2144	1942	1668	1374	1152
11	1498	1417	1425	1600	2156	2160	2166	2141	1933	1657	1366	1146
12	1496	1416	1423	1600	2168	2160	2166	2139	1924	1647	1358	1140
13	1493	1414	1420	1600	2180	2202	2166	2139	1916	1638	1349	1132
14	1490	1412	1417	1600	2175	2256	2166	2139	1908	1627	1338	1126
15	1489	1408	1415	1602	2173	2231	2166	2138	1900	1618	1329	1120
16	1487	1406	1414	1604	2170	2208	2172	2132	1891	1608	1320	1112
17	1486	1404	1420	1606	2168	2195	2188	2125	1882	1597	1314	1106
18	1484	1402	1430	1606	2168	2190	2178	2120	1874	1587	1307	1100
19	1482	1420	1441	1606	2166	2188	2173	2114	1864	1578	1300	1094
20	1480	1440	1468	1606	2164	2185	2171	2109	1856	1568	1292	1087
21	1477	1463	1475	1612	2163	2182	2168	2102	1845	1558	1284	1082
22	1474	1464	1482	1618	2162	2182	2168	2096	1834	1547	1275	1078
23	1470	1465	1487	1622	2161	2182	2168	2090	1824	1536	1266	1074
24	1466	1465	1491	1710	2161	2182	2168	2084	1816	1524	1257	1072
25	1462	1465	1495	1826	2161	2182	2166	2078	1807	1512	1250	1070
26	1458	1464	1498	1880	2161	2182	2164	2070	1797	1500	1240	1068
27	1455	1463	1500	1908	2160	2180	2160	2062	1788	1490	1232	1066
28	1452	1461	1510	1920	2160	2178	2158	2055	1777	1482	1226	1064
29	1448	1458	1540	1938	---	2176	2157	2048	1767	1474	1220	1060
30	1444	1456	1550	1946	---	2175	2156	2040	1756	1465	1214	1056
31	1440	---	1560	1954	---	2174	---	2031	---	1456	1206	---
MAKS.	1517	1465	1562	1564	2180	2256	2188	2156	2022	1746	1448	1198
MIN.	1438	1400	1414	1956	1958	2158	2156	2027	1751	1452	1202	1055
ORTALAMA	1485	1433	1460	1670	2111	2178	2167	2114	1892	1604	1324	1121

YILLIK ORT.:1712 cm.

8 - BATI AKDENIZ HAVZASI

08132 - ÇAYBOGAZI BARAJI-GÖMBE

YERİ : (29° 41' 0" D - 36° 31' 43" K) Gömbe-KaŞ karayolundan 1 km. Gidilerek çayboğazı barajına varılır.

YAĞIŞ ALANI : 38.4 Km2 YAKLAŞIK KOT : 1189.9 m.

GÖZLEM SÜRESİ :01/10/1997 - 30/09/2006

EN YÜKSEK VE EN DÜŞÜK SEVİYELER:

2006 Su yılında en yüksek seviye	:	2923	cm.	01/06/2006
2006 Su yılında en düŞük seviye	:	150	cm.	04/10/1905
Gözlem süresinde en yüksek seviye	:	3215	cm.	15/05/2002
Gözlem süresinde en düŞük seviye	:	677	cm.	15/10/2001

GÖZLEM SÜRESİNDE ORTALAMA SEVİYE : 2017 cm.

SEVİYELER 1 EKİM 1905 'DEN 30 EYLÜL 2006 'A KADAR CM. OLARAK

GUN/AY	EKİM	KASIM	ARALIK	OCAK	ŞUBAT	MART	NİSAN	MAYIS	HAZİRAN	TEMMUZ	AĞUSTOS	EYLÜL
1	346	567	822	901	1242	1600	2074	2525	2923	2595	2170	1310
2	295	578	824	900	1257	1610	2096	2543	2934	2587	2154	1273
3	241	588	824	900	1274	1621	2107	2557	2946	2580	2122	1236
4	150	597	826	916	1291	1632	2118	2571	2957	2573	2090	1200
5	170	606	828	923	1309	1642	2129	2585	2932	2570	2059	1163
6	190	614	830	931	1326	1653	2141	2600	2907	2566	2027	1127
7	210	627	831	939	1343	1654	2152	2614	2882	2563	1995	1090
8	232	631	831	947	1360	1675	2163	2628	2857	2556	1963	1046
9	256	642	832	955	1378	1686	2175	2642	2836	2550	1931	1002
10	244	653	832	963	1395	1647	2186	2656	2815	2544	1900	958
11	293	609	833	971	1412	1709	2197	2671	2794	2537	1874	914
12	314	684	833	979	1430	1732	2208	2685	2773	2530	1848	870
13	333	694	834	986	1447	1756	2220	2700	2752	2509	1822	841
14	354	701	835	994	1464	1780	2233	2714	2731	2488	1796	812
15	368	713	836	1002	1481	1793	2249	2728	2720	2470	1770	783
16	380	724	836	1010	1489	1810	2260	2740	2708	2451	1742	736
17	392	740	836	1025	1497	1826	2271	2751	2699	2433	1718	690
18	400	753	836	1039	1505	1843	2289	2763	2689	2414	1695	643
19	400	769	837	1054	1514	1859	2307	2774	2678	2397	1672	596
20	400	790	837	1069	1522	1876	2325	2786	2664	2378	1648	550
21	400	813	838	1083	1530	1892	2344	2797	2649	2360	1625	508
22	422	817	839	1098	1538	1909	2364	2809	2640	2342	1601	465
23	434	821	839	1112	1546	1925	2380	2820	2630	2323	1577	464
24	450	821	845	1127	1554	1942	2398	2832	2620	2305	1554	462
25	476	821	850	1142	1563	1958	2416	2843	2610	2287	1531	460
26	488	821	856	1156	1572	1975	2434	2855	2600	2269	1508	458
27	504	821	863	1171	1582	1991	2452	2867	2588	2251	1484	456
28	518	821	871	1185	1591	2008	2470	2878	2592	2233	1460	454
29	530	821	876	1200	---	2024	2489	2890	2596	2217	1425	468
30	543	822	882	1214	---	2041	2507	2901	2600	2202	1393	482
31	555	---	892	1218	---	2057	---	2912	---	2186	1351	---
MAKS.	560	822	895	1233	1594	2064	2514	2917	2923	2595	2170	1310
MIN.	150	567	822	900	1242	1600	2074	2525	2588	2180	1351	454
ORTALAMA	364	715	841	1035	1443	1810	2271	2730	2744	2427	1758	783

YILLIK ORT.:1578 cm.

9 - ANTALYA HAVZASI

09071 - KORKUTELİ BARAJI GÖL RASATI

YERİ : (30° 9' 0" D - 37° 5' 0" K) KORKUTELİ İLÇESİNE 4 KM MESAFEDEKİ KORKUTELİ BARAJI GÖLÜNDEDİR.

YAĞIŞ ALANI : 261.4 Km2 YAKLAŞIK KOT : 1041.52 m.

GÖZLEM SÜRESİ :01/11/1976 - 30/09/2006

EN YÜKSEK VE EN DÜŞÜK SEVİYELER:

2006 Su yılında en yüksek seviye	:	3124	cm.	01/06/2006
2006 Su yılında en düşük seviye	:	0	cm.	15/09/2006
Gözlem süresinde en yüksek seviye	:	2869	cm.	03/06/2002
Gözlem süresinde en düşük seviye	:	0	cm.	01/09/1993

GÖZLEM SÜRESİNDE ORTALAMA SEVİYE : 1490 cm.

SEVİYELER 1 EKİM 1905 'DEN 30 EYLÜL 2006 'A KADAR CM. OLARAK

GUN/AY	EKİM	KASIM	ARALIK	OCAK	ŞUBAT	MART	NİSAN	MAYIS	HAZİRAN	TEMMUZ	AĞUSTOS	EYLÜL
1	1178	1326	1478	1568	1668	1762	1883	2000	2124	1835	1328	562
2	1182	1330	1481	1571	1671	1765	1886	2004	2125	1817	1306	532
3	1190	1334	1484	1574	1674	1768	1889	2008	2126	1799	1294	502
4	1194	1340	1487	1577	1677	1771	1892	2011	2127	1782	1271	472
5	1198	1343	1490	1580	1679	1774	1895	2015	2128	1764	1248	444
6	1205	1347	1493	1583	1682	1777	1899	2020	2129	1756	1224	412
7	1210	1351	1495	1586	1685	1780	1902	2024	2129	1748	1200	374
8	1215	1355	1495	1590	1688	1783	1905	2029	2129	1742	1180	334
9	1220	1359	1496	1594	1693	1788	1908	2034	2129	1737	1159	294
10	1225	1362	1497	1597	1698	1791	1910	2039	2128	1732	1138	260
11	1229	1366	1498	1600	1703	1794	1913	2043	2127	1728	1115	228
12	1234	1370	1499	1603	1707	1798	1917	2047	2127	1712	1092	196
13	1238	1375	1500	1606	1711	1805	1921	2053	2111	1698	1070	158
14	1242	1380	1502	1609	1714	1812	1924	2053	2098	1688	1050	118
15	1246	1385	1507	1612	1717	1818	1927	2065	2084	1675	1030	80
16	1250	1390	1510	1615	1720	1822	1936	2068	2065	1662	1012	0
17	1260	1395	1513	1618	1723	1825	1940	2071	2049	1647	994	0
18	1264	1402	1516	1621	1726	1828	1943	2074	2036	1627	976	0
19	1268	1409	1519	1624	1728	1831	1947	2077	2018	1607	954	0
20	1272	1416	1522	1628	1730	1834	1950	2080	2001	1587	927	0
21	1276	1422	1525	1632	1733	1838	1954	2083	1983	1565	900	0
22	1280	1428	1536	1636	1736	1842	1957	2086	1968	1542	871	0
23	1284	1435	1535	1640	1739	1845	1964	2088	1954	1519	842	0
24	1288	1441	1540	1644	1742	1848	1970	2091	1936	1498	812	0
25	1292	1446	1544	1648	1745	1851	1974	2093	1918	1476	782	0
26	1296	1452	1547	1651	1748	1855	1977	2096	1899	1454	750	6
27	1302	1460	1552	1654	1753	1860	1980	2113	1885	1434	718	10
28	1308	1464	1555	1657	1758	1865	1985	2116	1878	1414	686	14
29	1312	1468	1559	1660	---	1869	1992	2118	1866	1394	654	18
30	1317	1473	1562	1663	---	1875	1996	2120	1849	1373	622	22
31	1322	---	1565	1666	---	1875	---	2122	---	1351	592	---
MAKS.	1324	1475	1566	1666	1759	1880	1997	2122	3124	1835	1328	562
MIN.	1178	1326	1478	1568	1668	1762	1883	2000	1845	1344	582	0
ORTALAMA	1251	1394	1516	1616	1712	1817	1934	2062	2037	1624	993	167

YILLIK ORT.:1511 cm.

18 - SEYHAN HAVZASI

18-15 - SEYHAN BARAJI GÖL

YERİ :(35° 20' 53" D - 37° 2' 21" K) SEYHAN BARAJI GÖLÜNDEDİR.

YAĞIŞ ALANI : 19250 Km2 YAKLAŞIK KOT : 73 m.

GÖZLEM SÜRESİ :01/10/1994 - 30/09/2006

EN YÜKSEK VE EN DÜŞÜK SEVİYELER:

2006 Su yılında en yüksek seviye	:	6580	cm.	12/05/2006
2006 Su yılında en düşük seviye	:	5604	cm.	21/09/2006
Gözlem süresinde en yüksek seviye	:	6759	cm.	24/04/1995
Gözlem süresinde en düşük seviye	:	5182	cm.	04/03/1997

GÖZLEM SÜRESİNDE ORTALAMA SEVİYE : 6137 cm.

SEVİYELER 1 EKİM 1905 'DEN 30 EYLÜL 2006 'A KADAR CM. OLARAK

GUN/AY	EKİM	KASIM	ARALIK	OCAK	ŞUBAT	MART	NİSAN	MAYIS	HAZİRAN	TEMMUZ	AĞUSTOS	EYLÜL
1	5899	5862	6043	6212	6344	6278	6504	6549	6474	6405	6126	6014
2	5892	5864	6043	6229	6332	6283	6500	6561	6467	6387	6112	5996
3	5880	5865	6045	6246	6318	6277	6508	6570	6468	6381	6110	5977
4	5884	5863	6047	6260	6293	6273	6514	6571	6457	6377	6112	5959
5	5884	5868	6042	6275	6264	6258	6520	6571	6446	6374	6115	5939
6	5873	5875	6043	6282	6253	6255	6526	6570	6447	6372	6112	5922
7	5870	5876	6042	6289	6255	6256	6532	6565	6448	6371	6113	5902
8	5858	5885	6042	6293	6258	6262	6526	6561	6447	6373	6116	5889
9	5848	5895	6040	6301	6257	6275	6517	6563	6449	6371	6123	5869
10	5840	5905	6038	6292	6256	6287	6510	6565	6450	6374	6126	5849
11	5849	5916	6035	6290	6265	6301	6505	6564	6440	6371	6130	5827
12	5853	5921	6033	6293	6274	6314	6500	6580	6442	6370	6127	5809
13	5851	5923	6029	6294	6271	6324	6495	6555	6442	6368	6126	5787
14	5849	5920	6027	6293	6271	6322	6487	6546	6443	6363	6126	5765
15	5851	5920	6026	6295	6270	6323	6480	6543	6443	6352	6125	5740
16	5845	5922	6033	6298	6277	6329	6470	6538	6442	6339	6131	5716
17	5834	5929	6035	6311	6278	6340	6478	6541	6440	6333	6139	5692
18	5832	5934	6037	6312	6276	6351	6496	6537	6426	6322	6142	5665
19	5837	5942	6039	6323	6264	6356	6506	6531	6429	6315	6134	5641
20	5844	5956	6052	6326	6264	6362	6510	6527	6430	6308	6133	5623
21	5839	5956	6067	6321	6267	6387	6519	6523	6433	6301	6138	5604
22	5848	5966	6076	6314	6271	6401	6530	6520	6445	6297	6170	5620
23	5849	5974	6090	6314	6273	6413	6527	6521	6437	6282	6177	5646
24	5841	5992	6103	6314	6280	6423	6526	6514	6431	6283	6164	5662
25	5845	6003	6117	6325	6280	6434	6526	6511	6421	6265	6147	5671
26	5852	6011	6138	6335	6269	6447	6530	6505	6419	6247	6128	5676
27	5855	6018	6151	6341	6271	6462	6535	6496	6421	6227	6108	5674
28	5857	6014	6169	6350	6274	6470	6539	6481	6417	6207	6088	5672
29	5857	6027	6181	6343	---	6477	6543	6478	6416	6185	6072	5678
30	5861	6040	6192	6348	---	6485	6542	6482	6411	6160	6051	5684
31	5857	---	6102	6352	---	6494	---	6480	---	6141	6032	---
MAKS.	5899	6040	6102	6352	6344	6494	6543	6580	6468	6405	6177	6014
MIN.	5832	5862	6026	6212	6253	6255	6470	6478	6411	6141	6032	5604
ORTALAMA	5855	5934	6069	6302	6275	6352	6513	6536	6439	6316	6121	5772

YILLIK ORT.:6208 cm.

BÖLÜM III

AKIM ANAHTARI OLMAYAN, ORTALAMA AZAMİ, ASGARİ VE MEVCUT AKIM ÖLÇÜLERİ VERİLEN İSTASYONLAR

01. Meriç-Ergene Havzasi
D01A001 MERIC N. KAPIKULE

YERİ: DOGAN HUDUT KARAKOLUNU GECIP KAPIKULE SEDDESINE CIKINCA AKISYONUNE TERS OLARAK 500M GIDILINCE ULASILIR. E16C1
26°22'12" Doğu - 41°42'38" Kuzey
YAĞIŞ ALANI: 24300.00 km2 YAKLAŞIK KOT: 38.51 m
GÖZLEM SÜRESİ: 01.01.1950 - 30.09.2006

01. Meriç-Ergene Havzasi
D01A004 MERİÇ N. ESKİKÖY

YERİ: ESKİKOY KOYUNU GECTIKTEN SONRA SINIR KARAKOLU'NUN BULUNDUGU YERDEKI DEMIRYOLU KOPRUSUNUN MEMBAINDA SOL SAHILDEDIR.
26°37'57" Doğu - 41°21'50" Kuzey
YAĞIŞ ALANI: 37471.00 km2 YAKLAŞIK KOT: 18 m
GÖZLEM SÜRESİ: 26.06.1956 - 30.09.2006

01. Meriç-Ergene Havzasi
D01A013 HAYRABOLU D. INECIK

YERİ: 1961TEKIRDAG-MALKARA YOLUNUN 21.KM.DEKI INECIK NAHIYESINDEDIR.
27°17'0" Doğu - 40°56'0" Kuzey
YAĞIŞ ALANI: 92.18 km2 YAKLAŞIK KOT: 146 m
GÖZLEM SÜRESİ: 01.01.1952 - 30.09.2006

01. Meriç-Ergene Havzasi
D01G047 ALTINYAZI BRJ. GÖL GÖZLEM

YERİ: 1987UZUNKÖPRÜ-KEŞAN YOLUNUN 19 KM SİNDEN SAĞA AYRILAN YOLUN 6 KMSİNDEKİ ALTINYAZI BARAJINDADIR.
26°34'0" Doğu-41°4'0" Kuzey
YAĞIŞ ALANI: 85.40 km2 YAKLAŞIK KOT: 38 m
GÖZLEM SÜRESİ: 01.10.1970 - 30.09.2006(34 Yıl)

01. Meriç-Ergene Havzasi
D01A052 MANİKA D. K.YONCALI

YERİ: SARAY-KÜÇÜKYONCALI KÖYÜNDEDİR. F19B2
27°58'0" Doğu - 41°24'0" Kuzey

YAĞIŞ ALANI: 118.30 km2 YAKLAŞIK KOT: 135 m
GÖZLEM SÜRESİ: 19.03.1976 - 30.09.2006

			ÖLÇÜLEN AKIMLAR		
EŞEL SEVİYESİ (CM)	AKIM(M3/SN)	TARİH	EŞEL SEVİYESİ (CM)	AKIM(M3/SN)	TARİH
83	1,662	14.02.2006	72	0,897	28.03.2006

01. Meriç-Ergene Havzasi
D01A058 ÇÖMLEKDERE ÇÖMLEKKÖY

YERİ: EDIRNE-COMLEKKOY ICINDEDIR. E17A4
26°36'31" Doğu - 41°50'38" Kuzey
YAĞIŞ ALANI: 65.50 km2 YAKLAŞIK KOT: 89 m
GÖZLEM SÜRESİ: 17.09.1986 - 30.09.2006

01. Meriç-Ergene Havzasi
D01A061 ÇESME D. AHMETBEY

YERİ: ÇEŞME DERE AHMETBEY YOLUNDADIR.
27°35'0" Doğu - 41°27'0" Kuzey
YAĞIŞ ALANI: 52.02 km2 YAKLAŞIK KOT: 120 m
GÖZLEM SÜRESİ: 06.01.1989 - 30.09.2006

			ÖLÇÜLEN AKIMLAR		
EŞEL SEVİYESİ (CM)	AKIM(M3/SN)	TARİH	EŞEL SEVİYESİ (CM)	AKIM(M3/SN)	TARİH
78	0,502	10.03.2006	51	0,036	05.04.2006

01. Meriç-Ergene Havzasi
D01A064 ÇAKMAK D. ÇAKMAK

YERİ: ÇAKMAKKÖY-HAMİTLİ KÖY YOLU 500 M SONRAKI KÖPRÜNÜN TAKRIBEN 100 M MANSABINDADIR.
26°40'30" Doğu - 41°22'20" Kuzey
YAĞIŞ ALANI: 85.00 km2 YAKLAŞIK KOT: 28 m
GÖZLEM SÜRESİ: 21.09.1989 - 30.09.2006

01. Meriç-Ergene Havzasi
D01A074 DEGİRMENDERE YENİCE

YERİ:
27°37'58" Doğu - 41°43'24" Kuzey
YAĞIŞ ALANI: 5.97 km2 YAKLAŞIK KOT: 390 m
GÖZLEM SÜRESİ: 30.11.2004 - 30.09.2006

01. Meriç-Ergene Havzasi
D01A075 KOCADERE K.OGUNLU

YERİ: Lalapaşa-Hanlıyenice yolu 150 deki köprü üzerindedir.
26°47'32" Doğu - 41°55'35" Kuzey
YAĞIŞ ALANI: 41.80 km2 YAKLAŞIK KOT: 474 m
GÖZLEM SÜRESİ:01.10.2005 -30.09.2006

			ÖLÇÜLEN AKIMLAR		
EŞEL SEVİYESİ (CM)	AKIM(M3/SN)	TARİH	EŞEL SEVİYESİ (CM)	AKIM(M3/SN)	TARİH

31	0,009	15.11.2005	43	0,122	24.04.2006
44	0,199	08.12.2005	42	0,115	28.04.2006
42	0,098	31.01.2006	38	0,033	26.05.2006
43	0,175	24.02.2006	37	0,029	16.06.2006
60	0,772	09.03.2006	32	0,008	14.07.2006

02. Marmara Havzasi

D02G025 B. ÇEKMECE GÖLÜ GÖL GÖZLEM

YERİ: B. ÇEKMECE BARAJI, DOLUSAVAK YANINDADIR. PAFTA 25.000: İST-F21-D4 28°33'35" Doğu-41°1'40" Kuzey
YAĞIŞ ALANI: 639.60 km2 YAKLAŞIK KOT: 1 m
GÖZLEM SÜRESİ: 24.06.1966 - 30.09.2006

02. Marmara Havzasi

D02A052 ÇINAR DERE Çelikgürü

YERİ: 1987BIGA-ÇANAKKALE KARAYOLU 21`İNCI KM.SİNDE ÇINARDERE KÖPRU-SU 20 M.MENBA`SINDADIR.
27°2'53" Doğu - 40°19'31" Kuzey
YAĞIŞ ALANI: 56.80 km2 YAKLAŞIK KOT: 31 m
GÖZLEM SÜRESİ: 01.10.1971 - 30.09.2006

ÖLÇÜLEN AKIMLAR

EŞEL SEVİYESİ (CM)	AKIM(M3/SN)	TARİH	EŞEL SEVİYESİ (CM)	AKIM(M3/SN)	TARİH
14	0.019	11.10.2005	19	0.050	08.05.2006
13	0.015	09.11.2005	19	0.165	13.06.2006
17	0.053	15.12.2005	17	0.033	24.07.2006
35	0.881	27.02.2006	17	0.025	17.08.2006
61	2.779	16.03.2006	25	0.207	12.09.2006
23	0.102	11.04.2006	18	0.106	27.09.2006

02. Marmara Havzasi

D02G054 MOLOVA ALİBEYKÖY BRJ

YERİ: ALİBEYKÖY BARAJI KULE İÇİNDE BULUNMAKTADIR. PAFTA 25.000: İST-F21-C3 28°55'21" Doğu-41°6'10" Kuzey
YAĞIŞ ALANI: 154.90 km2 YAKLAŞIK KOT: 50 m
GÖZLEM SÜRESİ: 14.03.1974 - 30.09.2006

02. Marmara Havzasi

D02G059 Atikhisar Brj. Göl Gözlem

YERİ: 26°53'10" Doğu-40°7'30" Kuzey
YAĞIŞ ALANI: 321.92 km2 YAKLAŞIK KOT: 37 m
GÖZLEM SÜRESİ: 01.06.1975 - 30.09.2006(29 Yıl)

02. Marmara Havzasi

D02A062 KAVAK DERESİ Kavak

YERİ: KEŞAN-GELİBOLU KARAYOLUNUN KAVAK KÖYÜ GIRIŞINDEKI KÖPRÜDEDIR.
26°53'10" Doğu - 40°37'28" Kuzey
YAĞIŞ ALANI: 723.53 km2 YAKLAŞIK KOT: 2 m
GÖZLEM SÜRESİ: 25.11.1976 - 30.09.2006

02. Marmara Havzasi

D02A066 Atikhisar Brj. Dolusavak

YERİ: ATIKHISAR BARAJI DOLUSAVAĞINDADIR.
26°31'20" Doğu - 40°7'38" Kuzey
YAĞIŞ ALANI: 321.92 km2 YAKLAŞIK KOT: 40 m
GÖZLEM SÜRESİ: 01.06.1978 - 30.09.2006

02. Marmara Havzasi

D02A086 Atikhisar Brj. Sol Ana Kan.

YERİ: ÇANAKKALE-ATIKHISAR BARAJI`NIN SOL ANAKANALINDADIR.
26°31'6" Doğu - 40°7'29" Kuzey
YAĞIŞ ALANI: 321.92 km2 YAKLAŞIK KOT: 40 m
GÖZLEM SÜRESİ: 01.06.1978 - 01.09.2006

02. Marmara Havzasi

D02A087 Atikhisar Brj. Sag Ana Kan.

YERİ: CANAKKALE-ATIKHISAR BARAJI`NIN SAG ANAKANALINDADIR.
26°31'8" Doğu - 40°7'44" Kuzey
YAĞIŞ ALANI: 321.92 km2 YAKLAŞIK KOT: 40 m
GÖZLEM SÜRESİ: 01.06.1978 - 30.09.2006

02. Marmara Havzasi

D02A089 K.Kumla D. Küçükkumla

YERİ: Bursa Gemlik ilçesinin küçükkumla köyünün üstündeki kırga-zinosunun yanındadır.
29°7'0" Doğu - 40°29'0" Kuzey
YAĞIŞ ALANI: 20.00 km2 YAKLAŞIK KOT: 52 m

GÖZLEM SÜRESİ: 17.09.1985 - 30.09.2006

ÖLÇÜLEN AKIMLAR

EŞEL SEVİYESİ (CM)	AKIM(M3/SN)	TARİH	EŞEL SEVİYESİ (CM)	AKIM(M3/SN)	TARİH
22	0,048	04.10.2005	33	0,355	19.04.2006
26	0,133	07.11.2005	30	0,217	12.05.2006
32	0,266	01.12.2005	29	0,177	13.06.2006
38	0,567	02.01.2006	23,50	0,062	14.07.2006
38,50	0,687	02.02.2006	20	0,013	15.08.2006
48	1,132	09.03.2006	22	0,012	15.09.2006

02. Marmara Havzasi

D02G109 Iznik G. Göl Göz.(Iznik Merkez)

YERİ: İZNİK DSİ TESİSLERİ İÇİNDEKİ İSKELEDEDİR.
40°25'48" Doğu-29°42'26" Kuzey
YAĞIŞ ALANI: 1235.00 km2 YAKLAŞIK KOT: 83.27 m
GÖZLEM SÜRESİ: 01.10.1990 - 30.09.2006(14 Yıl)

02. Marmara Havzasi

D02A121 BALİKLI ÇAYI ASAGİ INOVA

YERİ: AŞAĞIİNOVA KÖYÜNDEN YENİCE İSTİKAMETİNE 2KM. MESAFEDEKİ KÖPRÜNÜN 20 M. MANSABINDADIR.
27°17'39" Doğu - 40°5'1" Kuzey
YAĞIŞ ALANI: 188.40 km2 YAKLAŞIK KOT: 187 m
GÖZLEM SÜRESİ: 28.08.1995 - 30.09.2006

ÖLÇÜLEN AKIMLAR

EŞEL SEVİYESİ (CM)	AKIM(M3/SN)	TARİH	EŞEL SEVİYESİ (CM)	AKIM(M3/SN)	TARİH
18	0.053	26.10.2005	30	0.804	27.04.2006
28	0.309	25.11.2005	25	0.319	23.05.2006
25	0.285	07.12.2005	24	0.310	13.06.2006
38	1.118	18.01.2006	0	0.001	27.07.2006
67	7.678	27.02.2006	0	0.000	24.08.2006
63	4.960	13.03.2006	0	0.000	21.09.2006

02. Marmara Havzasi

D02A123 Kocadere Muratoba

YERİ: BURSA GEMLİK KARAYOLU ÜZERİNDE ENGÜRÜCÜK KÖYÜNE GİRMEDEN SA-ĞA SAPILIR.6 Km SONRA MURATOBA KÖYÜNÜN 1 Km MANSABINDA SAĞ
29°10'54" Doğu - 40°22'30" Kuzey
YAĞIŞ ALANI: 65.79 km2 YAKLAŞIK KOT: 92 m
GÖZLEM SÜRESİ: 01.10.1995 - 30.09.2006

02. Marmara Havzasi

D02G124 Iznik G. Göl Gözlem (Boyalica)

YERİ: ORHANGAZİ - İZNİK yolu üzerinde bulunan BOYALICA beldesibelediye binası karşısındadır.
29°32'0" Doğu-40°29'0" Kuzey
YAĞIŞ ALANI: 0.00 km2 YAKLAŞIK KOT: 83.41 m
GÖZLEM SÜRESİ: 01.10.1995 - 30.09.2006(9 Yıl)

02. Marmara Havzasi

D02A130 AYNA DERE ERDEK

YERİ: ERDEK İLÇESİNİN 2 KM. KUZEYINDEDIR.
27°48'42" Doğu - 40°24'40" Kuzey
YAĞIŞ ALANI: 5.73 km2 YAKLAŞIK KOT: 60 m
GÖZLEM SÜRESİ: 01.03.1997 - 30.09.2006

ÖLÇÜLEN AKIMLAR

EŞEL SEVİYESİ (CM)	AKIM(M3/SN)	TARİH	EŞEL SEVİYESİ (CM)	AKIM(M3/SN)	TARİH
13	0.011	11.11.2005	12	0.020	23.06.2006
13	0.018	09.12.2005	12	0.012	11.07.2006
49	0.378	22.02.2006	12	0.007	26.07.2006
57	0.251	22.03.2006	13	0.005	17.08.2006
48	0.070	24.04.2006	16	0.006	04.09.2006
14	0.031	02.06.2006	21	0.025	25.09.2006

02. Marmara Havzasi

D02G139 Yuvacik Brj. Göl Gözlem

YERİ: BURSA KOCAELİ KARAYOLUNUN YUVACIK SAPAĞINDAN DÖNÜLÜR.YUVACIKBELDESİNE GELİNİR İSTASYON YUVACIK BELDESİNİN 1.5 Km GÜNEYİNdedir.
29°58'21" Doğu-40°40'30" Kuzey
YAĞIŞ ALANI: 255.00 km2 YAKLAŞIK KOT: 122 m
GÖZLEM SÜRESİ: 16.12.1998 - 30.09.2005(6 Yıl)

02. Marmara Havzasi

D02A144 CEVİZDERE NAİPKÖY

YERİ: NAIPKOYUN GUNEYINDEKI MEZARLIK YOLUNU TAKIP EDEREK GIDEN ORMAN YOLUNUN YAKLASIK 2 KMSINDEDIR.G18B3
27°24'0" Doğu - 40°51'0" Kuzey
YAĞIŞ ALANI: 2.10 km2 YAKLAŞIK KOT: 55 m
GÖZLEM SÜRESİ: 02.12.2004 - 30.09.2006

02. Marmara Havzasi
D02A145 KÜÇÜKKÖY D. YESİLPINAR

YERİ: İSTANBUL İLİ GAZİOSMANPAŞA İLÇESİ -ALİBEYKÖY ARASINDAKİ KARAYOLU ÜZERİNDE YEŞİLPINAR MEVKİİNDEDİR. PAFTA 25.000:İST-F21-C3
28°55'10" Doğu - 41°4'3" Kuzey
YAĞIŞ ALANI: 15.30 km2 YAKLAŞIK KOT: 22 m
GÖZLEM SÜRESİ: 01.10.2005 - 30.09.2006

02. Marmara Havzasi
D02A146 AYAZAĞA D. AYAZAĞA

YERİ: İSTANBUL İLİ ŞİŞLİ İLÇESİ'NE BAĞLI AYAZAĞA KÖYÜ İÇİNDE BULUNMAKTADIR. PAFTA 25.000:İST-F21-C3
28°59'49" Doğu - 41°6'43" Kuzey
YAĞIŞ ALANI: 24.30 km2 YAKLAŞIK KOT: 14 m
GÖZLEM SÜRESİ: 02.10.2005 - 30.09.2006

02. Marmara Havzasi
D02A147 Uludere UMURBEY BRJ.ÇIKIŞI

YERİ: LAPSEKİ İLÇESİ UMURBEY BARAJI ÇIKIŞINDADIR.
26°39'57" Doğu - 40°14'32" Kuzey
YAĞIŞ ALANI: 278.20 km2 YAKLAŞIK KOT: 25 m
GÖZLEM SÜRESİ: 05.09.2005 - 30.09.2006

			ÖLÇÜLEN AKIMLAR		
EŞEL SEVİYESİ (CM)	AKIM(M3/SN)	TARİH	EŞEL SEVİYESİ (CM)	AKIM(M3/SN)	TARİH
0	0.000	11.10.2005	17	0.214	10.05.2006
25	1.932	29.11.2005	13	0.068	14.06.2006
24	0.695	23.12.2005	14	0.045	24.07.2006
0	0.875	16.02.2006	0	0.000	23.08.2006
0	0.311	31.03.2006	0	0.000	11.09.2006
18	0.421	19.04.2006	13	0.101	27.09.2006

02. Marmara Havzasi
D02A148 ALİBEYKÖY D. ALİBEYKÖY

YERİ: İSTANBUL İLİ EYÜP İLÇESİ'NE BAĞLI ALİBEYKÖY İÇİNDEKİ KARAYOLU KÖPRÜSÜ ÜZERİNDEDİR. PAFTA 25.000:İST-F21-C3
28°56'56" Doğu - 41°4'59" Kuzey
YAĞIŞ ALANI: 16.20 km2 YAKLAŞIK KOT: 5 m
GÖZLEM SÜRESİ: 03.10.2005 - 30.09.2006

03. Susurluk Havzasi
D03A004 Kille (Aliova) Ç. Deveci Konagi

YERİ: Bursa-Mustafakemalpaşa bucağındaki köprünün mansabındadır.
28°34'0" Doğu - 39°55'0" Kuzey
YAĞIŞ ALANI: 4888.00 km2 YAKLAŞIK KOT: 61.50 m
GÖZLEM SÜRESİ: 01.09.1980 - 30.09.2006

03. Susurluk Havzasi
D03A017 BEDİR Ç. ÇAVDARHİSAR

YERİ: KÜTAHYA GEDİZ YOLU'NUN 58. KM'SİNDEKİ ÇAVDARHİSAR İLÇESİ İÇERİSİNDE BULUNAN KÖPRÜNÜN 30 M. MENMASIDIR.
29°36'49" Doğu - 39°11'54" Kuzey
YAĞIŞ ALANI: 147.40 km2 YAKLAŞIK KOT: 1018 m
GÖZLEM SÜRESİ: 16.04.1966 - 30.09.2006

03. Susurluk Havzasi
D03A020 KOCADERE AKÇAŞEHİR

YERİ: TAVŞANLI'YA GELİNIR.SOLDAN STABLIZE YOLA GIRILEREK DEMIRYOLUNU GEÇINCE ÖRENCIK YOLUNA GIRILIR. AKÇAŞEHIR YOLUNUN KARŞI SAHILINDEDIR.
29°36'34" Doğu - 39°25'53" Kuzey
YAĞIŞ ALANI: 1082.70 km2 YAKLAŞIK KOT: 873 m
GÖZLEM SÜRESİ: 01.12.1963 - 30.09.2006

03. Susurluk Havzasi
D03A027 Gölbasi G. Çikis

YERİ: BURSA-YENİŞEHIR YOLUNUN 22 KM SİNDEN SOLA AYRILAN HAM YOLDAN 2 KM SONRAKI GÖLBAŞI GÖLÜ ÇIKIŞINDADIR.
29°19'6" Doğu - 40°13'21" Kuzey
YAĞIŞ ALANI: 64.30 km2 YAKLAŞIK KOT: 119 m
GÖZLEM SÜRESİ: 01.03.1968 - 30.09.2006

03. Susurluk Havzasi
D03A028 Aksu D. Gölbasi Gölü Giris

YERİ: BURSA-YENİŞEHİR YOLUNUN 22.Km SİNDEKİ KÖPRÜDEDİR.
29°19'10" Doğu - 40°12'51" Kuzey
YAĞIŞ ALANI: 50.70 km2 YAKLAŞIK KOT: 192 m
GÖZLEM SÜRESİ: 01.11.1968 - 30.09.2006

03. Susurluk Havzasi
D03A029 Deliçay Kan. Panayirköprü
YERİ: BURSA-YALOVA YOLUNDA GİRİLEREK PANAYIR MAHALLESİNE VARILIR.İSTASYON KÖPRÜ ÜZERİNDEDİR.
40°14'32" Doğu - 29°4'21" Kuzey
YAĞIŞ ALANI: 537.00 km2 YAKLAŞIK KOT: 100 m
GÖZLEM SÜRESİ: 01.10.2000 - 30.09.2006

03. Susurluk Havzasi
D03G036 ÇAYGÖREN BARAJI Göl Gözlem
YERİ: 28°13'5" Doğu-39°16'23" Kuzey
YAĞIŞ ALANI: 1510.00 km2 YAKLAŞIK KOT: 240 m

03. Susurluk Havzasi
D03G037 Gölbasi G. Göl Gözlem
YERİ: Bursa yenişehir yolunun 22.Km.sinden sola ayrılan yolun 1750 M.sindeki gölbaşı gölündedir.
29°19'0" Doğu-40°13'0" Kuzey
YAĞIŞ ALANI: 64.30 km2 YAKLAŞIK KOT: 120 m
GÖZLEM SÜRESİ: 16.01.1970 - 30.09.2005(33 Yıl)

03. Susurluk Havzasi
D03A038 Kirkpinarlar D. Uludag
YERİ: ULUDAĞ YOLUNUN 37 KM SİNDEKI ÇOBAN KAYA MEVKIINDE DONBAY ÇUKURUNUN SAĞ AYAĞINDADIR.
29°8'55" Doğu - 40°7'22" Kuzey
YAĞIŞ ALANI: 8.30 km2 YAKLAŞIK KOT: 1675 m
GÖZLEM SÜRESİ: 01.11.1971 - 30.09.2005

03. Susurluk Havzasi
D03A041 ÇAYGÖREN BARAJI Dip Savak
YERİ: SINDIRGI-ÇAYGÖREN BARAJININ DİPSAVAĞIN 50 M MANSABINDADIR.
28°12'43" Doğu - 39°16'33" Kuzey
YAĞIŞ ALANI: 1510.00 km2 YAKLAŞIK KOT: 225 m
GÖZLEM SÜRESİ: 01.12.1975 - 30.09.2006

03. Susurluk Havzasi
D03A042 ÇAYGÖREN BARAJI SOL ANAKANAL
YERİ: SINDIRGI-ÇAYGÖREN BRJ. ÇIKIŞINDAKİ, SOL ANAKANAL ÜZERINDEDIR.
28°12'41" Doğu - 39°16'19" Kuzey
YAĞIŞ ALANI: 1510.00 km2 YAKLAŞIK KOT: 225 m
GÖZLEM SÜRESİ: 01.07.1975 - 30.09.2006

03. Susurluk Havzasi
D03G047 KARA DERE MANYAS GÖLÜ - ERGİLI REGÜLATÖR ÇIKIŞI
YERİ: MANYAS GÖLÜNÜ BOŞALTAN KARADERE ÜSTÜNDE ERGİLİ KÖYÜKÖPRÜSÜNDE.
28°2'56" Doğu-40°7'52" Kuzey
YAĞIŞ ALANI: 3049.00 km2 YAKLAŞIK KOT: 13.55 m
GÖZLEM SÜRESİ: 01.12.1977 - 30.09.2006(3 Yıl)

03. Susurluk Havzasi
D03A049 Cuma D. Cumayeri
YERİ: BURSA ORHANELİ KAZASININ BÜYÜKORHAN YOLUNUN 26.KM.SİNDEKİCUMAYERİ KÖPRÜSÜNÜN 100 M MANSABINDADIR.
29°0'0" Doğu - 39°49'0" Kuzey
YAĞIŞ ALANI: 127.20 km2 YAKLAŞIK KOT: 650 m
GÖZLEM SÜRESİ: 01.07.1979 - 30.09.2006

03. Susurluk Havzasi
D03G063 MANYAS GÖLÜ KOCAGÖL (GÖL GÖZLEM)
YERİ: MANYAS KOCAGÖL KÖYÜNDEDİR.
27°50'41" Doğu-40°9'53" Kuzey
YAĞIŞ ALANI: 3351.80 km2 YAKLAŞIK KOT: 14 m

03. Susurluk Havzasi
D03A073 Emet Ç. Gökçedag
YERİ: BURSA-ORHANELİ-DURSUNBEY YOLUNUNGÖKÇEDAĞ MEVKİİNDEKİ
28°59'0" Doğu - 39°36'0" Kuzey
YAĞIŞ ALANI: 2500.00 km2 YAKLAŞIK KOT: 350 m
GÖZLEM SÜRESİ: 28.09.1984 - 30.09.2006

03. Susurluk Havzasi
D03A075 Nilüfer Ç. Doganci Brj.Çikis
YERİ: BURSA-ORHANELİ YOLU ÜZERİNDEKİ S.SAYGI DOĞANCI BARAJININ200 m. MANSABINDADIR.
28°58'5" Doğu - 40°7'16" Kuzey
YAĞIŞ ALANI: 446.90 km2 YAKLAŞIK KOT: 250 m
GÖZLEM SÜRESİ: 01.01.1984 - 30.09.2006

03. Susurluk Havzasi
D03G077 Doganci Brj. Göl Gözlem

YERİ: BURSA-ORHANELİ YOLUNUN 20.KM.SİNDEKİ DOĞANCI BARAJINDAKİDOLUSAVAK YAKININDADIR.
28°58'0" Doğu-40°7'0" Kuzey
YAĞIŞ ALANI: 450.00 km2 YAKLAŞIK KOT: 312 m
GÖZLEM SÜRESİ: 01.10.1984 - 30.09.2005(21 Yıl)

03. Susurluk Havzasi
D03G079 Kuruçay Göleti Göl Gözlem

YERİ: 29°3'0" Doğu-39°28'0" Kuzey
GÖZLEM SÜRESİ: 01.10.1984 - 30.09.2006(19 Yıl)

03. Susurluk Havzasi
D03G080 Kayabogazi Brj. Göl Gözlem

YERİ: 29°37'0" Doğu-39°25'0" Kuzey
YAĞIŞ ALANI: ---- km2 YAKLAŞIK KOT: 907 m
GÖZLEM SÜRESİ: 01.10.1984 - 30.09.2006(18 Yıl)

03. Susurluk Havzasi
D03A086/A Adalı Ark

YERİ: Adalı köyünün 1 km. güneyindeki köprünün 20 metre menbasında sağ sahildedir.
28°15'33" Doğu - 39°24'07" Kuzey
YAĞIŞ ALANI: 63.00 km2 YAKLAŞIK KOT: 375 m
GÖZLEM SÜRESİ: 01.09.1987 - 30.09.2006

03. Susurluk Havzasi
D03A087 KOCABÜK DERESİ YESİLOVA

YERİ: MERKEZ YEŞİOLAVA KÖYÜNDEN MANYASA GIDEN YOLUN 2. KM'SINDEKI KÖPRÜDEDIR.
27°57'37" Doğu - 39°54'18" Kuzey
YAĞIŞ ALANI: 142.00 km2 YAKLAŞIK KOT: 250 m
GÖZLEM SÜRESİ: 15.06.1998 - 30.09.2006

ÖLÇÜLEN AKIMLAR

EŞEL SEVİYESİ (CM)	AKIM(M3/SN)	TARİH	EŞEL SEVİYESİ (CM)	AKIM(M3/SN)	TARİH
29	0.007	05.10.2005	54	1.221	24.03.2006
32	0.018	07.11.2005	46	0.507	13.04.2006
35	0.086	08.12.2005	40	0.221	08.05.2006
38	0.275	06.01.2006	31	0.023	06.06.2006
66	2.364	16.02.2006	30	0.018	29.06.2006

03. Susurluk Havzasi
D03G093 MANYAS GÖLÜ GÖLYAKA

YERİ: Manyas gölü gölyaka köyü E.İ.E nin göl gözlem istasyonunun bitişiğindedir.
27°52'30" Doğu-40°11'0" Kuzey
YAĞIŞ ALANI: 3022.40 km2 YAKLAŞIK KOT: 14.31 m
GÖZLEM SÜRESİ: 01.10.1990 - 30.09.2006(7 Yıl)

03. Susurluk Havzasi
D03G097 Çavdarhisar Brj. Göl Gözlem

YERİ: 29°35'0" Doğu-39°10'0" Kuzey
YAĞIŞ ALANI: ---- km2 YAKLAŞIK KOT: 1033 m
GÖZLEM SÜRESİ: 08.02.1991 - 30.09.2006(12 Yıl)

03. Susurluk Havzasi
D03A100 Susurluk Ç. Canbolu

YERİ: BURSA İLİ KARACABEY İLÇESİNİN 500 M GÜNEYİNDEKİ ANA KÖPRÜÜZERİNDEDİR.
28°21'10" Doğu - 28°11'50" Kuzey
YAĞIŞ ALANI: 7009.00 km2 YAKLAŞIK KOT: 8 m
GÖZLEM SÜRESİ: 01.10.1994 - 30.09.2006

03. Susurluk Havzasi
D03A108 Karadere Pasalar

YERİ: M.K.PAŞA ORGANİZE SANAYİ YOLUNDAN 8 KM.SONRA PAŞALAR KÖYÜNEVARILIR.İSTASYON KÖYÜN ALTINDA KARAYOLU KÖPRÜSÜNDEDİR.
39°58'23" Doğu - 28°17'57" Kuzey
YAĞIŞ ALANI: 86.51 km2 YAKLAŞIK KOT: 95 m
GÖZLEM SÜRESİ: 19.08.1996 - 30.09.2006

03. Susurluk Havzasi
D03A112 EĞRİ (SIĞIRCI) DERE DOGRUCA

YERİ: Karacabey-Bandırma karayolunun Bandırma ya 3 Km kala sola
28°1'46" Doğu - 40°16'48" Kuzey
YAĞIŞ ALANI: 144.00 km2 YAKLAŞIK KOT: 27 m
GÖZLEM SÜRESİ: 01.10.1996 - 30.09.2006

03. Susurluk Havzasi
D03G114 Ulubat G. Göl Göz.(Eskikaraagaç)

YERİ: Bursa Karacabey yolunun 40 km sinde Eskikaraağaç köyündedir.

28°36'45" Doğu-40°11'9" Kuzey
YAĞIŞ ALANI: 10.56 km2 YAKLAŞIK KOT: 2 m
GÖZLEM SÜRESİ: 01.06.1997 - 30.09.2005(8 Yıl)

03. Susurluk Havzasi
D03A119 DEGİRMEN D. ÖRENLİ SIMAV

YERİ: SİMAV ÖRENLİ MEVKİİNDEDİR.
28°52'0" Doğu - 39°12'0" Kuzey
YAĞIŞ ALANI: 396.00 km2 YAKLAŞIK KOT: 835 m
GÖZLEM SÜRESİ: 26.06.1998 - 30.09.2006

ÖLÇÜLEN AKIMLAR

EŞEL SEVİYESİ (CM)	AKIM(M3/SN)	TARİH	EŞEL SEVİYESİ (CM)	AKIM(M3/SN)	TARİH
1	0.015	27.10.2005	12	0.211	26.01.2006
2	0.019	17.11.2005	17	0.564	23.02.2006
10	0.089	14.12.2005	0	0.026	25.11.2005

03. Susurluk Havzasi
D03G122 Yenice Göleti Göl Gözlem

YERİ: 29°9'0" Doğu-39°18'0" Kuzey
YAĞIŞ ALANI: ---- km2 YAKLAŞIK KOT: 1123 m

03. Susurluk Havzasi
D03G123 Çerte Göleti Göl Gözlem

YERİ: 29°28'0" Doğu-39°15'0" Kuzey
YAĞIŞ ALANI: ---- km2 YAKLAŞIK KOT: 1191 m

03. Susurluk Havzasi
D03G124 MANYAS GÖLÜ BEREKETLİ-ESKI BALIKHANE

YERİ: İSTASYON BANDIRMA-BEREKETLİ KÖYÜNÜN 2 KM DOĞUSUNDA, ETİBANK POMPAJ TESISLERI YANINDA,ESKI BALIKHANE ISKELESINDEDIR.
27°59'7" Doğu-40°14'25" Kuzey
YAĞIŞ ALANI: 3351.80 km2 YAKLAŞIK KOT: 14.50 m
GÖZLEM SÜRESİ: 25.12.1998 - 30.09.2006(6 Yıl)

03. Susurluk Havzasi
D03A125 Emet Ç. Düğüncüler

YERİ: Gökçedağ tren istasyonu -Dursunbey Karayolunun 20.kmsindensağa sapılarak Dursunbey çayı boyunca kuzeye doğru ilerlenir
28°43'53" Doğu - 39°41'57" Kuzey
YAĞIŞ ALANI: 4365.00 km2 YAKLAŞIK KOT: 261 m
GÖZLEM SÜRESİ: 01.10.1999 - 30.09.2006

03. Susurluk Havzasi
D03A126 Sögütalan D. Güller

YERİ: M.K.Paşa ilçesi Çaltılıbük nahiyesi yolu üzerinden mezarlıkyanından sola sapılarak Güller köyüne varılır. İstasyon kö-
28°32'53" Doğu - 40°1'3" Kuzey
YAĞIŞ ALANI: 39.30 km2 YAKLAŞIK KOT: 161 m
GÖZLEM SÜRESİ: 01.06.1999 - 30.09.2006

03. Susurluk Havzasi
D03G127 Ulubat G. Göl Gözl.(Halilbey)

YERİ: 28°36'14" Doğu-40°10'42" Kuzey
YAĞIŞ ALANI: 10555 km2 YAKLAŞIK KOT: 2 m
GÖZLEM SÜRESİ:

03. Susurluk Havzasi
D03A128 SİMAV ÇAYI KADİKÖY KÖPRÜSÜ

YERİ: BİGADIÇ-KADIKÖYDEN BOR MADENİ OCAKLARINA GİDEN YOL ÜZERİNDEKİ SIMAV ÇAYI KÖPRÜSÜNDEDİR.
28°7'12" Doğu - 39°27'29" Kuzey
YAĞIŞ ALANI: 2271.50 km2 YAKLAŞIK KOT: 125.13 m
GÖZLEM SÜRESİ: 01.10.2004 - 30.09.2006

ÖLÇÜLEN AKIMLAR

EŞEL SEVİYESİ (CM)	AKIM(M3/SN)	TARİH	EŞEL SEVİYESİ (CM)	AKIM(M3/SN)	TARİH
22	3.807	14.10.2005	30	4.499	08.05.2006
76	72.670	10.03.2006	23	6.357	02.06.2006
48	28.391	10.04.2006	57	8.548	19.07.2006

03. Susurluk Havzasi
D03G137 IKİZCETEPELER BARAJI İKİZCETEPELER (GÖL GÖZLEM)

YERİ: BALIKESİR-MERKEZ İKIZCETEPELER BARAJINDADIR.
27°56'29" Doğu-39°29'29" Kuzey
YAĞIŞ ALANI: 469.50 km2 YAKLAŞIK KOT: 149 m

03. Susurluk Havzasi
D03A142 Uzun D. Arttiranlar

YERİ:
29°15'45" Doğu - 39°39'10" Kuzey
YAĞIŞ ALANI: 23.48 km2 YAKLAŞIK KOT: 1965 m
GÖZLEM SÜRESİ: 01.04.2004- 30.09.2006

03. Susurluk Havzasi
D03A143 Taskisla D. Arttiranlar

YERİ:
29°15'02" Doğu - 39°38'59" Kuzey
YAĞIŞ ALANI: 15.28 km2 YAKLAŞIK KOT: 792 m
GÖZLEM SÜRESİ: 01.04.2004- 30.09.2006

04. Kuzey Ege Havzasi
D04A035 KOCADERE MİSVAK

YERİ: AYVACIK-SÜLEYMANLI KÖYÜ İLE MISVAK KÖYÜ ARASINDAKI KÖPRÜDEDIR.
26°27'1" Doğu - 39°39'51" Kuzey
YAĞIŞ ALANI: 43.50 km2 YAKLAŞIK KOT: 135 m
GÖZLEM SÜRESİ: 01.10.1986 - 30.09.2006

			ÖLÇÜLEN AKIMLAR		
EŞEL SEVİYESİ (CM)	AKIM(M3/SN)	TARİH	EŞEL SEVİYESİ (CM)	AKIM(M3/SN)	TARİH
24	0.025	27.10.2005	25	0.381	01.02.2006
96	7.966	24.11.2005	42	1.060	20.03.2006
32	0.467	28.11.2005	32	0.297	13.04.2006
29	0.289	30.11.2005	27	0.220	11.05.2006
24	0.135	16.12.2005	24	0.195	12.06.2006
29	0.245	22.12.2005	20	0.070	10.07.2006

04. Kuzey Ege Havzasi
D04A038 KARAKOÇ DERESİ BOĞAZBAHÇE

YERİ: ALTINOVA BELDESİNIN 6 KM KUZEYINDE BOĞAZBAHÇE MEVKIINDEDIR.
26°47'36" Doğu - 39°16'1" Kuzey
YAĞIŞ ALANI: 46.21 km2 YAKLAŞIK KOT: 27 m
GÖZLEM SÜRESİ: 01.10.1995 - 30.09.2006

			ÖLÇÜLEN AKIMLAR		
EŞEL SEVİYESİ (CM)	AKIM(M3/SN)	TARİH	EŞEL SEVİYESİ (CM)	AKIM(M3/SN)	TARİH
0	0.005	14.10.2005	11	0.317	24.03.2006
4	0.027	12.12.2005	9	0.124	05.04.2006
8	0.088	04.01.2006	7	0.071	03.05.2006
8	0.045	09.02.2006	7	0.068	01.06.2006
9	0.176	07.03.2006	0	0.000	05.07.2006

04. Kuzey Ege Havzasi
D04A041 ILICA DERESI ZEYTİNLİ

YERİ: BAYRAMİÇ-ZEYTINLI KÖYÜNÜN 8 KM KUZEYINDEDIR.
26°31'15" Doğu - 39°53'29" Kuzey
YAĞIŞ ALANI: 50.80 km2 YAKLAŞIK KOT: 160 m
GÖZLEM SÜRESİ: 04.03.1999 - 30.09.2006

			ÖLÇÜLEN AKIMLAR		
EŞEL SEVİYESİ (CM)	AKIM(M3/SN)	TARİH	EŞEL SEVİYESİ (CM)	AKIM(M3/SN)	TARİH
0	0.014	06.10.2005	0	0.115	12.04.2006
0	0.015	10.11.2005	0	0.050	03.05.2006
0	0.043	12.12.2005	0	0.065	15.06.2006
0	0.160	20.01.2006	0	0.000	11.07.2006
0	0.125	15.02.2006	0	0.001	14.08.2006
31	0.534	17.03.2006	0	0.003	18.09.2006

04. Kuzey Ege Havzasi
D04A042 MANASTIR ÇAYI KAVLAKLAR

YERİ: EDREMİT KAVLAKLAR ILE AVCILAR KÖYLERI ARASINDAKI (KRİSTAL) MADEN SUYU IŞLETMESI ÖNÜNDEKI KÖPRÜDEDIR.
26°49'49" Doğu - 39°35'16" Kuzey
YAĞIŞ ALANI: 32.00 km2 YAKLAŞIK KOT: 55 m
GÖZLEM SÜRESİ: 01.10.2000 - 30.09.2006

			ÖLÇÜLEN AKIMLAR		
EŞEL SEVİYESİ (CM)	AKIM(M3/SN)	TARİH	EŞEL SEVİYESİ (CM)	AKIM(M3/SN)	TARİH
27	0.172	12.10.2005	36	0.914	03.05.2006
27	0.163	11.11.2005	31	0.535	29.05.2006
53	3.433	01.12.2005	27	0.293	27.06.2006
40	1.712	30.01.2006	26	0.185	11.07.2006
67	7.508	15.03.2006	23	0.008	31.08.2006
42	1.546	11.04.2006	23	0.048	11.09.2006

04. Kuzey Ege Havzasi
D04A044 GEYİKLİDERE MAZILI

YERİ: BERGAMA DİKİLİ YOLUNUN DİKİLİ'YE 9 KM KALA MAZILI KÖYÜ SAPAĞINDAN 5 KM SONRAKİ KARAYOLU KÖPRÜSÜ ÜZERİNDEDİR.(PAFTA J18 D1)
26°57'52" Doğu - 39°6'25" Kuzey
YAĞIŞ ALANI: 74.60 km2 YAKLAŞIK KOT: 59 m
GÖZLEM SÜRESİ: 05.12.2000 - 30.09.2006

			ÖLÇÜLEN AKIMLAR		
EŞEL SEVİYESİ (CM)	AKIM(M3/SN)	TARİH	EŞEL SEVİYESİ (CM)	AKIM(M3/SN)	TARİH
26	0,029	15.11.2005	36	0,499	17.02.2006
29	0,071	12.12.2005	45	1,917	10.03.2006
37	0,877	04.01.2006	33	0,390	21.04.2006
38	0,614	20.01.2006	31	0,117	09.06.2006

04. Kuzey Ege Havzasi
D04A048 BAKIRÇAY EGRİGÖL KÖP.

YERİ: İZMİR BERGAMA KARAYOLUNUN 90.KM SİNDEDİR.(PAFTA 18)
27°6'40" Doğu - 39°3'13" Kuzey
YAĞIŞ ALANI: 2940.00 km2 YAKLAŞIK KOT: 20 m
GÖZLEM SÜRESİ: 01.07.2003 - 30.09.2006

04. Kuzey Ege Havzasi
D04A049 BAKIRÇAY GÖÇBEYLİ

YERİ: BERGAMANIN GÖÇBEYLİ KASABASINI 1 KM GEÇTİKTEN SONRA BAKIRÇAY KÖPRÜSÜ ÜZERİNDEDİR.(PAFTA J18)
27°25'23" Doğu - 39°8'49" Kuzey
YAĞIŞ ALANI: 1407.60 km2 YAKLAŞIK KOT: 55 m
GÖZLEM SÜRESİ: 01.07.2003 - 30.09.2006

			ÖLÇÜLEN AKIMLAR		
EŞEL SEVİYESİ (CM)	AKIM(M3/SN)	TARİH	EŞEL SEVİYESİ (CM)	AKIM(M3/SN)	TARİH
29	1,241	29.12.2005	51	7,537	02.03.2006

04. Kuzey Ege Havzasi
D04A050 HASANDERE ÇAMAVLU

YERİ: KOZAK ÇAMAVLU KARAYOLUNUN HASANDERESİNİ KESTİĞİ KÖPRÜNÜN MENBAĞINDADIR.(PAFTA J18-A3)
27°8'20" Doğu - 39°18'45" Kuzey
YAĞIŞ ALANI: 22.70 km2 YAKLAŞIK KOT: 476 m
GÖZLEM SÜRESİ: 01.10.2003 - 30.09.2006

			ÖLÇÜLEN AKIMLAR		
EŞEL SEVİYESİ (CM)	AKIM(M3/SN)	TARİH	EŞEL SEVİYESİ (CM)	AKIM(M3/SN)	TARİH
34	0,073	05.12.2005	56	1,254	16.03.2006
43	0,368	14.02.2006	39	0,255	26.04.2006
55	0,938	07.03.2006	34	0,088	06.06.2006

04. Kuzey Ege Havzasi
D04A055 HAVRAN ÇAYI HAVRAN BARAJ ÇIKIŞI

YERİ: HAVRAN BARAJININ 200 M MANSABINDAKİ KÖPRÜDEDIR.
27°10'3" Doğu - 39°34'17" Kuzey
YAĞIŞ ALANI: 187.50 km2 YAKLAŞIK KOT: 77 m
GÖZLEM SÜRESİ: 01.10.2004 - 30.09.2006

			ÖLÇÜLEN AKIMLAR		
EŞEL SEVİYESİ (CM)	AKIM(M3/SN)	TARİH	EŞEL SEVİYESİ (CM)	AKIM(M3/SN)	TARİH
91	0.626	23.12.2005	115	1.206	30.03.2006
149	14.673	19.01.2006	103	0.495	19.04.2006
103	2.618	03.02.2006	92	0.149	31.05.2006
108	3.237	09.02.2006	78	0.070	04.07.2006
155	14.052	03.03.2006	75	0.044	21.07.2006
136	4.110	07.03.2006	72	0.013	07.08.2006

04. Kuzey Ege Havzasi
D04A056 MADRA ÇAYI MADRA BARAJ ÇIKIŞI

YERİ: MADRA BARAJININ 500 M MANSABINDAKİ KÖPRÜDEDIR.
26°49'49" Doğu - 39°14'0" Kuzey
YAĞIŞ ALANI: 420.20 km2 YAKLAŞIK KOT: 37 m

05. Gediz Havzasi
D05G005 Marmara G. Göl Gözlem

YERİ: SALİHLI GÖLMARMARA YOLUNUN 20KM. DEN SULAMA KANALINA AYRILAN YOLUN 6KM SINDEDIR.K20 28°3'0" Doğu-38°35'32" Kuzey
YAĞIŞ ALANI: 225.70 km2 YAKLAŞIK KOT: 70 m
GÖZLEM SÜRESİ: ------ - 30.10.2006

05. Gediz Havzasi
D05A007 MARMARA G. REGÜLATÖR ÇIKIŞ

YERİ: SALİHLİNİN ADALA BUCAĞINA 26 KM MESAFEDEKİ REGÜLATÖRÜN MANSABINDADIR.(K20-A4)
28°3'5" Doğu - 38°35'30" Kuzey
YAĞIŞ ALANI: 255.70 km2 YAKLAŞIK KOT: 70 m
GÖZLEM SÜRESİ: 10.02.1959 - 30.09.2006

05. Gediz Havzasi
D05A015 MEDAR Ç. MEDAR KÖPRÜSÜ

YERİ: AKHİSAR SOMA YOL AYRIMINDAN SONRA 500 METRESİNDEKİ KÖPRÜDEDİR.(PAFTA K19-B1)
27°49'40" Doğu - 38°57'10" Kuzey
YAĞIŞ ALANI: 512.30 km2 YAKLAŞIK KOT: 106 m
GÖZLEM SÜRESİ: 16.08.1965 - 30.09.2006

05. Gediz Havzasi
D05A021 TABAK DERE ÇALTILI

YERİ: SALİHLİ TURGUTLU YOLUNUN 8 KM.DEKİ ÇALTILI KÖYÜNÜN ÇAMUR KAPLICALARI YOLUNUN 2.5 KM.DEDİR. L20
28°3'1" Doğu - 38°27'55" Kuzey
YAĞIŞ ALANI: 81.10 km2 YAKLAŞIK KOT: 137 m

GÖZLEM SÜRESİ: 16.04.1969 - 30.09.2006

ÖLÇÜLEN AKIMLAR

EŞEL SEVİYESİ (CM)	AKIM(M3/SN)	TARİH	EŞEL SEVİYESİ (CM)	AKIM(M3/SN)	TARİH
12	0,137	31.10.2005	17	0,460	15.12.2005
16	0,493	29.11.2005	42	3,671	27.02.2006
12	0,137	30.10.2005	26	6,619	16.03.2006

05. Gediz Havzasi

D05A025 GEDİZ N. MURADİYE KÖPRÜSÜ

YERİ: MANİSA'YA 9 KM MESAFEDEKİ MURADİYE KÖPRÜSÜNDEDİR.(PAFTA K18-C1)
27°20'3" Doğu - 38°40'57" Kuzey
YAĞIŞ ALANI: 15848.00 km2 YAKLAŞIK KOT: 17 m
GÖZLEM SÜRESİ: 01.02.1968 - 30.09.2006

ÖLÇÜLEN AKIMLAR

EŞEL SEVİYESİ (CM)	AKIM(M3/SN)	TARİH	EŞEL SEVİYESİ (CM)	AKIM(M3/SN)	TARİH
472	124,869	15.02.2006	262	50,130	02.03.2006

05. Gediz Havzasi

D05A028 GÖRDES Ç. HACIHIDIR

YERİ: SALİHLİ YUKARIPOYRAZ-HACIHIDIR YOLUNU TAKİBEN GÖRDES ÇAYI KÖPRÜSÜNE VARILIR.İSTASYON YERİ KÖPRÜDEDİR.(PAFTA K20-A3)
28°11'51" Doğu - 38°46'20" Kuzey
YAĞIŞ ALANI: 808.20 km2 YAKLAŞIK KOT: 305 m
GÖZLEM SÜRESİ: 01.06.1977 - 30.09.2006

ÖLÇÜLEN AKIMLAR

EŞEL SEVİYESİ (CM)	AKIM(M3/SN)	TARİH	EŞEL SEVİYESİ (CM)	AKIM(M3/SN)	TARİH
95	10,636	24.02.2006	128	30,316	16.03.2006

05. Gediz Havzasi

D05A031 ALASEHİR Ç. TAYTAN KÖP.

YERİ: SALİHLİ ANKARA KARAYOLUNUN 3.KM.SİNDEN SOLA SAPILIR. 2 KM.SONRA ALAŞEHİR ÇAYI TAYTAN KÖPRÜSÜNÜN 100 M. MEMBAĞINDADIR.(K20-03)
28°11'31" Doğu - 38°30'38" Kuzey
YAĞIŞ ALANI: 2513.00 km2 YAKLAŞIK KOT: 91 m
GÖZLEM SÜRESİ: 01.04.1981 - 30.09.2006

ÖLÇÜLEN AKIMLAR

EŞEL SEVİYESİ (CM)	AKIM(M3/SN)	TARİH	EŞEL SEVİYESİ (CM)	AKIM(M3/SN)	TARİH
80	3,529	30.11.2005	104	9,587	20.02.2006
39	0,631	12.12.2005	106	11,194	17.03.2006

05. Gediz Havzasi

D05A033 GEDİZ N. URGANLI

YERİ: TURGUTLU ANKARA ASFALTININ 14.KM.SİNDEN SOLA AYRILAN URGANLI İÇMELER YOLUNUN GEDİZ NEHRİ ÜZERİNDEKİ KÖPRÜDEDİR.(K19)
27°50'23" Doğu - 38°33'41" Kuzey
YAĞIŞ ALANI: 9587.00 km2 YAKLAŞIK KOT: 50 m
GÖZLEM SÜRESİ: 01.10.1982 - 30.09.2006

ÖLÇÜLEN AKIMLAR

EŞEL SEVİYESİ (CM)	AKIM(M3/SN)	TARİH	EŞEL SEVİYESİ (CM)	AKIM(M3/SN)	TARİH
108	5,736	28.12.2005	252	42,349	14.02.2006

05. Gediz Havzasi

D05A034 GÖRDES Ç. MADEN ÇESMESİ

YERİ: AKHİSAR GÖLMARMARA KARAYOLUNUN 20.KM SİNDEKİ SELENDİ GÖLÜNDEN SOLA SAPILIR, 9.KM DEN SONRA İSTASYONA VARILIR.(PAFTA K19-B3)
27°57'57" Doğu - 38°45'44" Kuzey
YAĞIŞ ALANI: 1444.00 km2 YAKLAŞIK KOT: 129 m
GÖZLEM SÜRESİ: 01.10.1982 - 30.09.2006

ÖLÇÜLEN AKIMLAR

EŞEL SEVİYESİ (CM)	AKIM(M3/SN)	TARİH	EŞEL SEVİYESİ (CM)	AKIM(M3/SN)	TARİH
128	0,063	25.10.2005	148	1,843	26.12.2005
127	0,071	15.11.2005	172	13,320	24.03.2006

05. Gediz Havzasi

D05A038 NİF Ç. HACIHALİLLER

YERİ: MANİSA TURGUTLU KARAYOLUNUN 15.KM SİNDEN SOLA AYRILAN YOLUN 1.KM SİNDEKİ KÖPRÜDEDİR. (K19-D4)
27°34'31" Doğu - 38°34'46" Kuzey
YAĞIŞ ALANI: 854.00 km2 YAKLAŞIK KOT: 36 m
GÖZLEM SÜRESİ: 01.10.1986 - 30.09.2006

05. Gediz Havzasi

D05G045 Gümele Göleti Göl Gözlem

YERİ: Gümele Gölü üzerindedir.
29°14'0" Doğu-38°58'0" Kuzey

05. Gediz Havzasi

D05A046 CONBULAT D. GÜMELE

YERİ: GEDİZ İLÇESI GÜMELE BELDESINDE GÜMELE BARAJ ÇIKIŞI
29°28'10" Doğu - 38°55'47" Kuzey
YAĞIŞ ALANI: 74.00 km2 YAKLAŞIK KOT: 790 m
GÖZLEM SÜRESİ: 15.12.1994 - 30.09.2006

05. Gediz Havzasi

D05G051 GÖLCÜK GÖLÜ GÖL GÖZLEM

YERİ: ÖDEMİŞ GÖLCÜK BELDESİNDEDİR.(PAFTA L20-A4)

28°1'30" Doğu-38°19'20" Kuzey
YAĞIŞ ALANI: 7.27 km2 YAKLAŞIK KOT: 1047.86 m
GÖZLEM SÜRESİ: 01.10.1997 - 30.09.2006(3 Yıl)

05. Gediz Havzasi
D05A054 DELİCEDERE ÇAMÖNÜ

YERİ: AKHİSAR ÇAMÖNÜ KÖYYOLUNUN YAKLAŞIK 7KM SİNDE SAĞA AYRILAN TALİ YOLUN BİTİMİNDEKİ DELİCE DERE ÜZERİNDEDİR.PAFTA K19-B2, K20-A1
27°54'6" Doğu - 38°56'59" Kuzey
YAĞIŞ ALANI: 38.10 km2 YAKLAŞIK KOT: 172 m
GÖZLEM SÜRESİ: 01.10.2000 - 30.09.2006

ÖLÇÜLEN AKIMLAR

EŞEL SEVİYESİ (CM)	AKIM(M3/SN)	TARİH	EŞEL SEVİYESİ (CM)	AKIM(M3/SN)	TARİH
20	0,530	23.01.2006	8	0,039	26.12.2005
68	8,516	10.02.2006	18	0,432	08.02.2006
39	2,278	12.03.2006	24	0,849	15.03.2006
10	0,072	18.04.2006	17	0,386	22.03.2006
14	0,186	18.11.2005	8	0,023	18.05.2006

05. Gediz Havzasi
D05A057 AZMAK Ç. SOBRAN KÖPRÜSÜ

YERİ: ALAŞEHİRYEŞİLYURT YOL AYRIMINDAN 6.5 KM SONRA SOBRAN KÖPRÜSÜNÜN 600 METRE MANSABINDADIR.(PAFTA L21-A3)
28°38'15" Doğu - 38°20'27" Kuzey
YAĞIŞ ALANI: 1580.00 km2 YAKLAŞIK KOT: 165 m
GÖZLEM SÜRESİ: 23.07.2003 -30.09.2006

ÖLÇÜLEN AKIMLAR

EŞEL SEVİYESİ (CM)	AKIM(M3/SN)	TARİH	EŞEL SEVİYESİ (CM)	AKIM(M3/SN)	TARİH
27	0,184	15.02.2006	35	0,629	08.03.2006

05. Gediz Havzasi
D05G058 DEMİRKÖPRÜ BARAJI GÖL GÖZLEM

YERİ: SALİHLİ DEMİRCİ YOLUNUNU ÜZERİNDEDİR.(PAFTA K20-C4)
28°18'46" Doğu-38°36'53" Kuzey
YAĞIŞ ALANI: 6590.00 km2 YAKLAŞIK KOT: 244 m
GÖZLEM SÜRESİ: 01.10.2002 - 30.09.2006

05. Gediz Havzasi
D05A059 DEMİRKÖPRÜ BARAJI ÇIKIŞ

YERİ: ADALA BELDESİNDEN YATAK BOYUNCA MEMBAYA DOĞRU 2.KM İLERİDEDİR.(PAFTA K20-C4)
28°16'25" Doğu - 38°35'55" Kuzey
YAĞIŞ ALANI: 6679.00 km2 YAKLAŞIK KOT: 128 m
GÖZLEM SÜRESİ: 01.10.2002 - 30.09.2006

ÖLÇÜLEN AKIMLAR

EŞEL SEVİYESİ (CM)	AKIM(M3/SN)	TARİH	EŞEL SEVİYESİ (CM)	AKIM(M3/SN)	TARİH
4	0,247	29.12.2005	7	0,340	26.05.2006

05. Gediz Havzasi
D05A060 GEDİZ N. HAMİDİYE KÖPRÜSÜ

YERİ: SALİHLİ KULA KARAYOLUNDAN KULA'YA 8 KM KALA SANDAL KASABASINA GİRİLİR. 15 KM SONRA GEDİZ NEHRİ ÜZERİNDEKİ KÖPRÜDEDİR.(PAFTA K21-D1)
28°36'13" Doğu - 38°39'17" Kuzey
YAĞIŞ ALANI: 4074.70 km2 YAKLAŞIK KOT: 290 m
GÖZLEM SÜRESİ: 01.10.2002 - 30.09.2006

ÖLÇÜLEN AKIMLAR

EŞEL SEVİYESİ (CM)	AKIM(M3/SN)	TARİH	EŞEL SEVİYESİ (CM)	AKIM(M3/SN)	TARİH
140	46,494	14.02.2006	117	28,927	21.03.2006

05. Gediz Havzasi
D05A062 AĞILLIDERE DERELİÇAMKÖY

YERİ: ALAŞEHİR EŞME KARAYOLUNUN 26. KM SİNDEN SAĞA AYRILAN YOLDAN HİDAYETLER KÖYÜ İLE DERELİÇAMKÖY'Ü YOLUNUN ARASINDAKİ KÖPRÜDEDİR.
28°50'53" Doğu - 38°17'17" Kuzey
YAĞIŞ ALANI: 21.00 km2 YAKLAŞIK KOT: 655 m
GÖZLEM SÜRESİ: 01.10.2003 - 30.09.2006

06. Küçük Menderes Havzasi
D06A013 FALAKA Ç. FALAKA

YERİ: İZMİR ÖDEMİŞ YOLUNUN 80.KM.SİNDE FALAKA KÖYÜNE VARILIR.5.KM KUZEYİNDEKİ KARAPINAR KÖYÜNE GİDEN KÖPRÜDEDİR.(PAFTA L19-D2,C1)
27°44'33" Doğu - 38°13'47" Kuzey
YAĞIŞ ALANI: 83.00 km2 YAKLAŞIK KOT: 130 m
GÖZLEM SÜRESİ: 01.10.1979 - 30.09.2006

ÖLÇÜLEN AKIMLAR

EŞEL SEVİYESİ (CM)	AKIM(M3/SN)	TARİH	EŞEL SEVİYESİ (CM)	AKIM(M3/SN)	TARİH
53	0,693	01.03.2006	81	4,656	13.03.2006

06. Küçük Menderes Havzasi
D06A018 ARAPASTAN DERESİ DAVUTLAR

YERİ: AYDIN-DAVUTLAR BUCAĞINDA ARAPASTAN DERESİNİN,DAVUTLAR-AĞAÇLI KARAYOLUNU KESTİĞİ KÖPRÜNÜN 100M. MENBASINDADIR.
27°17'56" Doğu - 37°43'58" Kuzey
YAĞIŞ ALANI: 11.30 km2 YAKLAŞIK KOT: 63 m
GÖZLEM SÜRESİ: 01.09.1988 - 30.09.2006

ÖLÇÜLEN AKIMLAR

EŞEL SEVİYESİ (CM)	AKIM(M3/SN)	TARİH	EŞEL SEVİYESİ (CM)	AKIM(M3/SN)	TARİH
19	0,186	21.03.2006	16	0,079	09.02.2006

6	0,001	11.07.2006	15	0,053	21.04.2006
12	0,022	29.11.2005	13	0,037	16.05.2006
13	0,039	23.01.2006	8	0,006	26.06.2006

06. Küçük Menderes Havzasi

D06A022 HIRSIZ D. BARAJ GİRISI

YERİ: IZMIR ALAÇATI REISDERE KÖYÜNÜN 2 KM.SİNDE BARAJ GİRİSİNDEDİR.(PAFTA L16)
26°25'20" Doğu - 38°18'17" Kuzey
YAĞIŞ ALANI: 33.00 km2 YAKLAŞIK KOT: 28 m
GÖZLEM SÜRESİ: 01.10.1998 - 30.09.2006

06. Küçük Menderes Havzasi

D06A030 K.MENDERES N. ÖDEMİS

YERİ: ÖDEMİŞ ADAGİDE KARAYOLUNUN 8.KM SİNDEKİ KÖPRÜ ÜZERİNDEDİR.(PAFTA M18)
28°0'48" Doğu - 38°9'4" Kuzey
YAĞIŞ ALANI: 850.00 km2 YAKLAŞIK KOT: 119 m
GÖZLEM SÜRESİ: 01.10.2003 - 30.09.2006

06. Küçük Menderes Havzasi

D06A031 K.MENDERES N. MAHMUTLAR REGÜLATÖRÜ

YERİ: TORBALI TİRE KARAYOLUNUN 35.KM SİNDEN SOLA DÖNEN YOLUN 3.KM SİNDEKİ REGÜLATÖRDEDİR(PAFTA L19-D2)
27°38'58" Doğu - 38°8'23" Kuzey
YAĞIŞ ALANI: 1889.40 km2 YAKLAŞIK KOT: 49 m
GÖZLEM SÜRESİ: 01.10.2003 - 30.09.2006

06. Küçük Menderes Havzasi

D06A032 K.MENDERES N. SELÇUK

YERİ: SELCUK IZMIR KARAYOLUNUN SELÇUK A 4 KM KALA SAĞA AYRILAN YOLUN 30. METRESİNDE KÖPRÜDEDİR.PAFTA M18-B2)
27°23'7" Doğu - 37°57'52" Kuzey
YAĞIŞ ALANI: 3254.00 km2 YAKLAŞIK KOT: 14 m
GÖZLEM SÜRESİ: 01.10.2003 - 30.09.2006

07. Büyük Menderes Havzasi

D07G002 Isikli G. Göl Gözlem

YERİ: Çivril-Işıklı-Dinar yolunun 21.Km. sindeki ışıklı Reg.Menbaındadır.
29°49'44" Doğu-38°12'55" Kuzey
YAĞIŞ ALANI: 2957.00 km2 YAKLAŞIK KOT: 822.49 m

07. Büyük Menderes Havzasi

D07A007 ÇÜRÜKSU BÖCELİ REGÜLATÖRÜ

YERİ: 1986DENİZLİ-KAKLIK YOLUNUN 13.KM.DEKİ BÖCELİ REGÜLATÖRÜ SAHASINDA REGÜLATÖR MANSABINDADIR.
29°12'31" Doğu - 37°48'21" Kuzey
YAĞIŞ ALANI: 974.00 km2 YAKLAŞIK KOT: 273 m
GÖZLEM SÜRESİ: 19.10.1978 - 30.09.2006

			ÖLÇÜLEN AKIMLAR		
EŞEL SEVİYESİ (CM)	AKIM(M3/SN)	TARİH	EŞEL SEVİYESİ (CM)	AKIM(M3/SN)	TARİH
73	5,858	30.01.2006	24	0,841	10.04.2006
84	7,555	13.03.2006	16	0,259	26.09.2006

07. Büyük Menderes Havzasi

D07G024 Bafa G. Göl Gözlem

YERİ: SÖKE MİLAS KARAYOLUNDA BAFA GÖLÜ KENARINDA KOCAORMAN YAĞ FABRİKASI YANINDADIR.
27°29'10" Doğu-37°28'36" Kuzey
YAĞIŞ ALANI: 315.00 km2 YAKLAŞIK KOT: 2 m

07. Büyük Menderes Havzasi

D07A035 ÇİNE ÇAYI SÖĞÜTCÜK

YERİ: ÇİNE-MUĞLA YOLUNUN(ESKİ) 17.KM.DE ÇİNE ÇAYI ÜZERİNDEDİR.
28°07'0" Doğu - 37°30'0" Kuzey
YAĞIŞ ALANI: 1462.00 km2 YAKLAŞIK KOT: 152 m
GÖZLEM SÜRESİ: 20.07.1964 - 30.09.2006

07. Büyük Menderes Havzasi

D07A039 KAPIZ D. ALANGÜLLÜ

YERİ: GERMENCİK DAĞKARAAĞAÇ YOLUNUN 3.6 KM SİNDEKİ ALANGÜLLÜ KÖPRÜSÜNDEDİR.
27°37'0" Doğu - 37°53'0" Kuzey
YAĞIŞ ALANI: 90.50 km2 YAKLAŞIK KOT: 73 m
GÖZLEM SÜRESİ: 08.12.1964 - 30.09.2006

07. Büyük Menderes Havzasi

D07A049 KARADİREK Ç. BASAĞAÇ

YERİ: SANDIKLI-AFYON YOLUNUN 15 KM SİNDEKİ HAM YOLUN 1 KM SİNDEKİB AŞAĞAÇ KÖYÜNÜN 800 M MEMBAINDADIR.HARİTA PAFATA: K24-D3
30°12'29" Doğu - 38°35'31" Kuzey
YAĞIŞ ALANI: 270.80 km2 YAKLAŞIK KOT: 1000 m
GÖZLEM SÜRESİ: 27.07.1968 - 30.09.2006

07. Büyük Menderes Havzasi

D07A053 IŞIKLI PINARLARI TAHLİYE KANALI

YERİ: 1964 ÇİVRİLE 10.KM.MESAFEDEKİ IŞIKLI PN. TAHLİYE KANALINDADIR.
29°51'0" Doğu - 38°19'0" Kuzey

YAĞIŞ ALANI: 100.00 km2 YAKLAŞIK KOT: 829 m
GÖZLEM SÜRESİ: 01.12.1963 - 30.09.2006

07. Büyük Menderes Havzasi
D07A054 IŞIKLI PINARLARI SULAMA KANALI

YERİ: 1967 ÇİVRİL'E 10.KM. MESAFEDEKİ IŞIKLI PN. REG.NÜN 75.M. MANSABINDA
29°51'0" Doğu - 38°19'0" Kuzey
YAĞIŞ ALANI: 100.00 km2 YAKLAŞIK KOT: 829 m
GÖZLEM SÜRESİ: 20.05.1964 - 30.09.2006

			ÖLÇÜLEN AKIMLAR		
EŞEL SEVİYESİ (CM)	AKIM(M3/SN)	TARİH	EŞEL SEVİYESİ (CM)	AKIM(M3/SN)	TARİH
79	0,558	07.10.2005	100	1,511	05.06.2006
74	0,418	08.11.2005	106	1,189	06.07.2006
45	0,241	02.05.2006	110	1,190	10.08.2006

07. Büyük Menderes Havzasi
D07A062 BÜYÜK MENDERES N. KOÇARLI KÖPRÜSÜ

YERİ: AYDIN-KOÇARLI YOLUNUN 16.5 KM.DEKİ BÜYÜK MENDERES N. KÖPRÜSÜNDEDİR.
27°43'0" Doğu - 37°49'0" Kuzey
YAĞIŞ ALANI: 22653.00 km2 YAKLAŞIK KOT: 17 m
GÖZLEM SÜRESİ: 23.01.1968 - 30.09.2006

			ÖLÇÜLEN AKIMLAR		
EŞEL SEVİYESİ (CM)	AKIM(M3/SN)	TARİH	EŞEL SEVİYESİ (CM)	AKIM(M3/SN)	TARİH
235	67,702	31.03.2006	177	48,791	10.04.2006
477	230,307	13.02.2006	164	41,562	13.04.2006
304	96,625	21.02.2006	134	31,622	18.04.2006
338	107,275	22.03.2006	94	15,816	21.04.2006
289	87,411	27.03.2006	61	8,864	30.05.2006
235	67,702	30.03.2006	83	18,270	19.06.2006

07. Büyük Menderes Havzasi
D07G067 ÇAPALI G. GÖL GÖZLEM

YERİ: ISPARTADAN DİNARA VARILIR. DİNAR AFYON YOLUNU TAKİBEN 4 KM SONRA SAĞA SAPILARAK DDY KARAKUYU İSTASYONUNA VARILIR. İSTASYONUN 1 KM GÜNEYİNDEDİR.
19°39'0" Doğu-42°30'0" Kuzey
YAĞIŞ ALANI: 368.90 km2 YAKLAŞIK KOT: 1005.10 m
GÖZLEM SÜRESİ: 01.01.1968 - 30.09.2006

07. Büyük Menderes Havzasi
D07A084 Degirmendere Kirazli

YERİ: DAVUTLAR BELDESİ KIRAZLI KÖYÜ MEVKIINDEDIR.
27°19'0" Doğu - 37°50'0" Kuzey
YAĞIŞ ALANI: 27.50 km2 YAKLAŞIK KOT: 75 m
GÖZLEM SÜRESİ: 27.05.1983 - 26.05.2006

07. Büyük Menderes Havzasi
D07G086 Topçam Brj. Göl Gözlem

YERİ: İstasyona Ait Adres Bilgisi Girilmemiştir.
28°0'0" Doğu-37°41'0" Kuzey
YAĞIŞ ALANI: 271.60 km2 YAKLAŞIK KOT: 81 m

07. Büyük Menderes Havzasi
D07A107 CILIMBIZ DERESİ. İNCIRLIOVA

YERİ: INCIRLIOVA-IKIZDERE KOYU YOLUNUN 4KM DEN SOLA AYRILAN STABLİZE YOLUNDAN 1KM GIDILEREK IST.ULASILIR.
27°43'21" Doğu - 37°52'55" Kuzey
YAĞIŞ ALANI: 37.50 km2 YAKLAŞIK KOT: 60 m
GÖZLEM SÜRESİ: 01.10.1989 - 30.09.2006

			ÖLÇÜLEN AKIMLAR		
EŞEL SEVİYESİ (CM)	AKIM(M3/SN)	TARİH	EŞEL SEVİYESİ (CM)	AKIM(M3/SN)	TARİH
95	0,237	23.01.2006	100	1,413	13.02.2006

07. Büyük Menderes Havzasi
D07A108 KARGIN DERESİ. KÖPRÜALAN

YERİ: SÖKE-MİLAS KARAYOLUNUN 19KM SINDEN SARIKEMER-AFSAR-YEŞİLKÖY YOLUNDAN 22 KM SONRA KÖPRÜALAN KÖYÜ GİRİŞİNDEKİ KÖPRÜDEDİR.
27°31'29" Doğu - 37°33'41" Kuzey
YAĞIŞ ALANI: 30.00 km2 YAKLAŞIK KOT: 163 m
GÖZLEM SÜRESİ: 01.10.1989 - 30.09.2006

			ÖLÇÜLEN AKIMLAR		
EŞEL SEVİYESİ (CM)	AKIM(M3/SN)	TARİH	EŞEL SEVİYESİ (CM)	AKIM(M3/SN)	TARİH
76	9,209	10.02.2006	71	7,709	08.03.2006
56	5,389	10.02.2006	135	22,242	13.03.2006

07. Büyük Menderes Havzasi
D07A109 YALKI DERESİ. İNCİRLİOVA

YERİ: İNCİRLIOVA-GERMENCİK YOLUNUN 4KM SİNDEN, SAGA AYRILAN ERBEYLİ-ARZULAR KÖYÜ YOLUNDAN, 5KM GİDİLEREK ISTASYONA ULAŞILIR.
27°41'21" Doğu - 37°53'32" Kuzey
YAĞIŞ ALANI: 41.80 km2 YAKLAŞIK KOT: 120 m

GÖZLEM SÜRESİ: 01.10.1989 - 30.09.2006

			ÖLÇÜLEN AKIMLAR		
EŞEL SEVİYESİ (CM)	AKIM(M3/SN)	TARİH	EŞEL SEVİYESİ (CM)	AKIM(M3/SN)	TARİH
4	0,057	31.05.2006	44	5,816	08.03.2006
4	0,066	27.12.2005	4	0,105	26.04.2006
8	0,298	06.01.2006	4	0,057	30.05.2006
25	1,645	13.02.2006	4	0,004	23.06.2006
7	0,128	24.03.2006	4	0,140	29.09.2006

07. Büyük Menderes Havzasi
D07A111 KIZILCASUYU AFYON SANDIKLI

YERİ: ISPARTA-SANDIKLI DEVLET YOLUNU TAKİBEN SANDIKLIDAN HOCALARYOLU İLE SORGUN YOLUNU TAKİBEN KIZILCA KÖYÜNE VARILIR. KESTEL DERESİ ÜZERİNDE 7 KM SONRA İST. ULAŞILIR. HARİTA PAFTA NO: L24-A1
30°4'50" Doğu - 38°22'55" Kuzey
YAĞIŞ ALANI: 36.00 km2 YAKLAŞIK KOT: 1145 m
GÖZLEM SÜRESİ: 01.03.1990 - 30.09.2006

07. Büyük Menderes Havzasi
D07A112 ÇAPALI G. REG. ÇIKIŞI

YERİ: ISPARTA-AFYON DEVLET KARAYOLUNU TAKİBEN KARAKUYU KÖYÜNE VARILIR.TAKRİBEN 2 KM STABİLİZE YOLDAN İSTASYON GÖL REG. ÇIKIŞINDADIR. HARİTA PAFTA NO: L24-D3
30°13'5" Doğu - 38°4'3" Kuzey
YAĞIŞ ALANI: 368.90 km2 YAKLAŞIK KOT: 1005.10 m
GÖZLEM SÜRESİ: 20.12.1989 - 30.09.2006

07. Büyük Menderes Havzasi
D07A114 DELİÇAY KAZANDERE

YERİ: NAZILLI - KEMER BARAJI, YOLUNUN 34.KM, SINDEN, SAĞA AYRILAN YOLUN 2.KM, SİNDEKİ KAZANDERE KÖYÜ İÇERİSİNDEKİ KÖPRÜDEDİR..
28°22'45" Doğu - 37°37'19" Kuzey
YAĞIŞ ALANI: 87.30 km2 YAKLAŞIK KOT: 140 m
GÖZLEM SÜRESİ: 01.10.1990 - 30.09.2006

07. Büyük Menderes Havzasi
D07G116 AKÇAY- KEMER BARAJI

YERİ: AYDIN-BOZDOĞAN İLÇESİNDEN 30KM MESAFEDEKİ KEMER KEMER BARAJINDADIR.
28°31'31" Doğu-37°34'22" Kuzey
YAĞIŞ ALANI: 3067.20 km2 YAKLAŞIK KOT: 295 m

07. Büyük Menderes Havzasi
D07G117 Adigüzel Brj. Göl Gözlem

YERİ: DENİZLİ-GÜNEY İLÇESİNDEN 20.KM.MESAFEDEKİ ADIGÜZEL BARAJINDADIR.
29°12'30" Doğu-38°9'35" Kuzey
YAĞIŞ ALANI: 9006.00 km2 YAKLAŞIK KOT: 460 m

07. Büyük Menderes Havzasi
D07G118 Yaylakavak Brj. Göl Gözlem

YERİ: ADIN-ÇİNE-KARPUZLU YAYLAKAVAK BARAJINDADIR.
27°48'17" Doğu-37°34'41" Kuzey
YAĞIŞ ALANI: 183.50 km2 YAKLAŞIK KOT: 160 m

07. Büyük Menderes Havzasi
D07G119 ÇAPALI G. II GÖL GÖZLEM

YERİ: ISPARTA-AFYON KARA YOLUNU TAKİBEN ÇAPALI KÖYÜNÜ 2 KM GEÇTİKTEN SONRA ÇAPALI GÖLÜNE VARILIR İSTASYON ALABALIK ÇİFTLİĞİNİN KENARINDADIR.
30°16'49" Doğu-38°4'28" Kuzey
YAĞIŞ ALANI: 10.00 km2 YAKLAŞIK KOT: 1005 m
GÖZLEM SÜRESİ: 01.10.2004 - 30.09.2006

08. Bati Akdeniz Havzasi
D08A028 Esen Ç. Yapilar

YERİ: FETHİYE-KAŞ YOLUNUN 63. KM DEKİ KÖPRÜDEDİR.
29°19'0" Doğu - 36°22'0" Kuzey
YAĞIŞ ALANI: 2461.00 km2 YAKLAŞIK KOT: 9 m
GÖZLEM SÜRESİ: - 30.09.1998

08. Bati Akdeniz Havzasi
D08A054 KEMER D. OSMAN KALFALAR

YERİ: BURDUR ÇAVDIR SÖĞÜT YOLUNU TAKİBEN OSMAN KALFALAR YOLUNA GİRİLİR. İSTASYON KÖY ÇIKIŞINDAKİ KEMER DERESİ ÜZERİNDEDİR. HARİTA PAFTA NO: N23-C3
29°52'47" Doğu - 37°6'9" Kuzey
YAĞIŞ ALANI: 86.60 km2 YAKLAŞIK KOT: 1415 m
GÖZLEM SÜRESİ: 03.09.1965 - 30.09.2006

08. Bati Akdeniz Havzasi
D08A060 HAMZABEY D. GÖKÇELER

YERİ: MUĞLA-MİLAS-BODRUM YOLUNUN 16.KM SİNDEN SOLA AYRILAN YAKAKÖY YOLUNUN 6. KM SİNDEKİ GÖKÇELER KÖYÜ KÖPRÜSÜNDEDİR.
27°45'0" Doğu - 37°12'0" Kuzey
YAĞIŞ ALANI: 245.00 km2 YAKLAŞIK KOT: 45 m
GÖZLEM SÜRESİ: 01.10.1968 - 30.09.2006

08. Bati Akdeniz Havzasi
D08G066 GÖLHİSAR G. GÖL GÖZLEM

YERİ: GÖLHİSAR-TEFENNİ YOLUNUN 10. KM SİNDEN SAĞA SAPILARAK YAMADI KÖYÜNE VARILIR. KÖYDEN 3.5 KM SONRA İSTASYONA VARILIR 0°69'0" Doğu-4°24'0" Kuzey
YAĞIŞ ALANI: 4954.00 km2 YAKLAŞIK KOT: 940.24 m
GÖZLEM SÜRESİ: 05.06.1970 - 30.09.2006

08. Bati Akdeniz Havzasi
D08A069 SEKİ ÇAYI ÖREN REG-ÇIKIŞI

YERİ: Fethiye regülatörünün mansabındadır.
29°33'0" Doğu - 36°45'0" Kuzey
YAĞIŞ ALANI: ---- km2 YAKLAŞIK KOT: 200 m
GÖZLEM SÜRESİ: 25.03.1970 - 30.09.2006

08. Bati Akdeniz Havzasi
D08A071 AGVA DERESİ ASİBUCAK

YERİ: KEMER ASİBUCAK KÖY YOLUNU TAKİBEN 6 KM. SONRA AĞVA REĞÜLATÖRÜNE VARILIR.İSTASYON 1 KM.İLERIDEDİR.(PAFTA O25-D4)
30°30'31" Doğu - 36°35'41" Kuzey
YAĞIŞ ALANI: 119.20 km2 YAKLAŞIK KOT: 80 m
GÖZLEM SÜRESİ: 05.07.1973 - 30.09.2006

08. Bati Akdeniz Havzasi
D08A072 DALAMAN Ç. MEŞEBÜKÜ

YERİ: MUĞLA-KÖYCEĞİZ-ACIPAYAM YOLUNUN 80.KM SİNDEN SOLA AYRILAN TÜRK MADEN YOLU KÖPRÜSÜNÜN MANSABINDADIR.
36°58'0" Doğu - 29°0'0" Kuzey
YAĞIŞ ALANI: 4301.00 km2 YAKLAŞIK KOT: 208 m
GÖZLEM SÜRESİ: 19.09.1976 - 30.09.2006

08. Bati Akdeniz Havzasi
D08A074 DALAMAN Ç. SANDALCIK

YERİ: KÖYCEĞİZ'E 95KM. MESAFEDEKİ BEYOBA-AKKÖPRÜ-SU ÇATI MEVKİİNDEDİR.
37°5'0" Doğu - 29°5'0" Kuzey
YAĞIŞ ALANI: 3932.00 km2 YAKLAŞIK KOT: 594 m
GÖZLEM SÜRESİ: 18.09.1976 - 30.09.2001

			ÖLÇÜLEN AKIMLAR		
EŞEL SEVİYESİ (CM)	AKIM(M3/SN)	TARİH	EŞEL SEVİYESİ (CM)	AKIM(M3/SN)	TARİH
109	5,760	27.10.2005	102	4,215	24.05.2006
122	8,164	16.11.2005	126	8,941	30.06.2006
121	7,695	14.12.2005	93	3,253	21.07.2006
144	12,508	31.01.2006	74	2,409	31.08.2006
145	12,713	28.04.2006	117	6,941	29.09.2006

08. Bati Akdeniz Havzasi
D08A075 DEGİRMEN D. HİSARARDI

YERİ: TEFENNİ-GÖLHİSAR-ÇAVDIR-YAMADI YOLUNU TAKİBEN HİSARARDI KÖYÜNDEN 800 M. GERİDE TESİS EDİLMİŞTİR. HARİTA PAFTA NO: N23-D4
29°36'31" Doğu - 37°6'5" Kuzey
YAĞIŞ ALANI: 20.56 km2 YAKLAŞIK KOT: 960 m
GÖZLEM SÜRESİ: 01.10.1977 - 30.09.2006

08. Bati Akdeniz Havzasi
D08A085 Namnen Ç. Dögüsbelen

YERİ: KÖYCEĞİZDEN 10 KM SONRA DÖĞÜŞBELENE GELİNİR.2 KM MESAFEDEDİR.
28°34'0" Doğu - 36°59'0" Kuzey
YAĞIŞ ALANI: 580.00 km2 YAKLAŞIK KOT: 25 m
GÖZLEM SÜRESİ: 24.09.1980 - 30.09.1999

			ÖLÇÜLEN AKIMLAR		
EŞEL SEVİYESİ (CM)	AKIM(M3/SN)	TARİH	EŞEL SEVİYESİ (CM)	AKIM(M3/SN)	TARİH
	0,724	18.10.2005		1,685	26.12.2005
	4,497	21.11.2005		14,212	27.01.2006

08. Bati Akdeniz Havzasi
D08A097 DERİNCE D. DERİNCE

YERİ: MİLAS- SELİMİYE-DERİNCE KÖYÜNDEN YAKLAŞIK 3.KM SONRA İSTASYONA ULAŞILIR.
27°38'27" Doğu - 37°25'10" Kuzey
YAĞIŞ ALANI: 41.50 km2 YAKLAŞIK KOT: 70 m
GÖZLEM SÜRESİ: 01.07.1985 - 30.09.2006

			ÖLÇÜLEN AKIMLAR		
EŞEL SEVİYESİ (CM)	AKIM(M3/SN)	TARİH	EŞEL SEVİYESİ (CM)	AKIM(M3/SN)	TARİH
20	0,125	15.12.2005	48	2,964	08.03.2006
16	0,125	17.01.2006	19	0,153 1	9.04.2006
63	5,476	06.02.2006	16	0,125	09.05.2006

08. Bati Akdeniz Havzasi
D08A098 EŞENCE D. KIZILCAYIKIK

YERİ: MUĞLA-MİLAS'A 6KM.MESAFEDEKİ KIZICAYIKIK KÖYÜNDEDİR.
27°47'0" Doğu - 37°22'0" Kuzey
YAĞIŞ ALANI: 30.50 km2 YAKLAŞIK KOT: 25 m
GÖZLEM SÜRESİ: 29.01.1986 - 30.09.2006

			ÖLÇÜLEN AKIMLAR		
EŞEL SEVİYESİ (CM)	AKIM(M3/SN)	TARİH	EŞEL SEVİYESİ (CM)	AKIM(M3/SN)	TARİH
37	0,081	15.12.2005	69	2,914	08.03.2006
36	0,037	17.01.2006	37	0,073	19.04.2006
62	2,019	06.02.2006	32	0,002	09.05.2006

08. Bati Akdeniz Havzasi
D08A105 YAVANOLUK D. YK.DODURGA

YERİ: ACIPAYAM-YAZIR KASABASININ ÇIKIŞINDAN BAŞLAYAN ORMAN YOLUNUN 15KM .SİNDEDİR.
29°37'41" Doğu - 37°24'28" Kuzey
YAĞIŞ ALANI: 40.50 km2 YAKLAŞIK KOT: 1565 m
GÖZLEM SÜRESİ: 01.12.1987 - 30.09.2006

			ÖLÇÜLEN AKIMLAR		
EŞEL SEVİYESİ (CM)	AKIM(M3/SN)	TARİH	EŞEL SEVİYESİ (CM)	AKIM(M3/SN)	TARİH
16	0,452	22.03.2006	2	0,010	06.04.2006

08. Bati Akdeniz Havzasi
D08A107 BÜYÜK D. KARAHASANTAŞI KÖP.

YERİ: FETHİYE ALTINYAYLA YOLUNUN 80KM.SİNDEN SAĞA AYRILAN KARAHASANTAŞI KARAYOLUNDAKİ KÖPRÜDEDİR.
29°37'25" Doğu - 36°56'50" Kuzey
YAĞIŞ ALANI: 41.00 km2 YAKLAŞIK KOT: 1385 m
GÖZLEM SÜRESİ: 22.09.1987 - 30.09.2006

08. Bati Akdeniz Havzasi
D08A109 GEYİK SUYU NİF KÖYÜ

YERİ: FETHİYE-ÇAMELİ YOLUNUN 27.KM.SİNDEKİ NİF KÖYÜNDEDİR..
29°10'0" Doğu - 36°50'58" Kuzey
YAĞIŞ ALANI: 8.20 km2 YAKLAŞIK KOT: 1035 m
GÖZLEM SÜRESİ: 28.10.1987 - 30.09.2006

			ÖLÇÜLEN AKIMLAR		
EŞEL SEVİYESİ (CM)	AKIM(M3/SN)	TARİH	EŞEL SEVİYESİ (CM)	AKIM(M3/SN)	TARİH
58	0,041	14.08.2006	56	0,037	04.09.2006

08. Bati Akdeniz Havzasi
D08A110 Elmali D. Nif Köyü

YERİ: FETHİYE ÇAMELİ YOLUNUN 42. KM SINDEDIR.
29°11'0" Doğu - 36°50'0" Kuzey
YAĞIŞ ALANI: 7.10 km2 YAKLAŞIK KOT: 960 m
GÖZLEM SÜRESİ: 28.10.1987 - 26.05.2006

08. Bati Akdeniz Havzasi
D08A111 Alanli D. NİF KÖYÜ

YERİ: FETHİYE ÇAMELI YOLUNUN 39 KM SINDE SAĞ SAHILDEDIR.
29°11'0" Doğu - 36°49'0" Kuzey
YAĞIŞ ALANI: 6.50 km2 YAKLAŞIK KOT: 925 m
GÖZLEM SÜRESİ: 28.10.1987 - 26.05.2006

08. Bati Akdeniz Havzasi
D08G114 Geyik Brj. Göl Gözlem

YERİ: Geyik Barajı üzerindedir.
27°54'0" Doğu-37°24'0" Kuzey

08. Bati Akdeniz Havzasi
D08A115 KOCAALAN D. MARMARİS

YERİ: GÖKOVA-MARMARİS YOLU ÜZERİNDE MARMARİSE 15 KM.MESAFEDEKİ KÖPRÜNÜN 200 M.MENBASINDADIR..
28°17'15" Doğu - 36°57'11" Kuzey
YAĞIŞ ALANI: 89.00 km2 YAKLAŞIK KOT: 25 m
GÖZLEM SÜRESİ: 15.09.1988 - 30.09.2006

			ÖLÇÜLEN AKIMLAR		
EŞEL SEVİYESİ (CM)	AKIM(M3/SN)	TARİH	EŞEL SEVİYESİ (CM)	AKIM(M3/SN)	TARİH
27	2,404	09.02.2006	5	0,405	07.07.2006
18	1,310	03.03.2006	6	0,311	08.08.2006

08. Bati Akdeniz Havzasi
D08A118 KAZANDERE HİSARÖNÜ

YERİ: MARMARİS DATÇA YOLUNUN 18.KM SİNDEKİ KÖPRÜDEDİR..
28°10'3" Doğu - 36°49'41" Kuzey
YAĞIŞ ALANI: 46.20 km2 YAKLAŞIK KOT: 20 m
GÖZLEM SÜRESİ: 20.12.1990 - 30.09.2006

08. Bati Akdeniz Havzasi
D08G119 Mumcular Brj. Göl Gözlem

YERİ: Mumcular Barajı üzerindedir.
27°39'0" Doğu-37°7'0" Kuzey

08. Bati Akdeniz Havzasi
D08A120 Sariçay Geyik Brj. Giris

YERİ: Geyik Barajı mansabındadır.
27°53'0" Doğu - 37°26'0" Kuzey
YAĞIŞ ALANI: 46.30 km2 YAKLAŞIK KOT: 475 m
GÖZLEM SÜRESİ: 01.10.1990 - 26.05.2006

08. Bati Akdeniz Havzasi
D08A121 BATIŞ D. KARAOVA

YERİ: MİLAS-MUMCULAR-GÖKPINAR YOLUNDAN,SOLA AYRILAN STABLIZE YOLDAN 1KM GİDİLEREK ISTASYONA ULAŞILIR.
27°41'1" Doğu - 37°6'50" Kuzey
YAĞIŞ ALANI: 70.50 km2 YAKLAŞIK KOT: 66 m
GÖZLEM SÜRESİ: 01.11.1988 - 30.09.2006

			ÖLÇÜLEN AKIMLAR		
EŞEL SEVİYESİ (CM)	AKIM(M3/SN)	TARİH	EŞEL SEVİYESİ (CM)	AKIM(M3/SN)	TARİH
44	0,005	11.10.2005	72	0,324	10.02.2006
46	0,010	17.11.2005	87	1,817	15.03.2006
49	0,012	22.12.2005	61	0,126	06.04.2006
51	0,025	18.01.2006	58	0,074	05.05.2006

08. Bati Akdeniz Havzasi
D08G122 YAPRAKLI G. GÖL GÖZLEM

YERİ: BURDUR-GÖLHİSAR DEVLET YOLUNU TAKİBEN GÖLHİSARA VARILIR. GÖLHİSARDAN SONRA DİRMİL YOLU İLE ELMALI YURT YÖNÜNDE DEVAM EDİLEREK ASVALT YOLLA BARAJA VARILIR.
37°2'0" Doğu-29°27'0" Kuzey
YAĞIŞ ALANI: 452.00 km2 YAKLAŞIK KOT: 1035.55 m
GÖZLEM SÜRESİ: 20.11.1990 - 30.09.2006

08. Bati Akdeniz Havzasi
D08A128 OLUK D. TOPTAS

YERİ: ANTALYA-KUMLUCA KARAYOLU İSTIKAMETINDEN GIDILEREK ERENTEPE YOL AYRIMINDAN ERENTEPEYE DÖNÜLÜR.ERENTEPEDEN YAKLAŞIK 5 KM.SONRA İSTASYONA VARILIR.
30°21'17" Doğu - 36°25'16" Kuzey
YAĞIŞ ALANI: 23.98 km2 YAKLAŞIK KOT: 188 m
GÖZLEM SÜRESİ: 01.10.1997 - 30.09.2006

08. Bati Akdeniz Havzasi
D08G133 ÇAVDIR BRJ. GÖL GÖZLEM

YERİ: BURDUR-ÇAVDIR YOLUNU TAKİBEN ÇAVDIRA VARILIR. ÇAVDIRDAN 15 KM SONRA BAYIR KÖYÜNÜNE SAPILIR. ÇAKIRLAR KÖYÜNDEN ÇAVDIR BARAJINA VARILIR. İSTASYON GÖVDEDE KADEMELİ EŞELLİ TESİS EDİLMİŞTİR.
29°43'53" Doğu-37°4'28" Kuzey
YAĞIŞ ALANI: 112.40 km2 YAKLAŞIK KOT: 1110 m
GÖZLEM SÜRESİ: 01.10.1996 - 30.09.2006

08. Bati Akdeniz Havzasi
D08A141 FETAŞ HES-GİRİŞİ FETHİYE

YERİ: FETHİYE- MERKEZ ESENKÖYDEDİR..
29°12'11" Doğu - 36°37'24" Kuzey
YAĞIŞ ALANI: km2 YAKLAŞIK KOT: 176 m
GÖZLEM SÜRESİ: 01.01.2000 - 30.09.2006

08. Bati Akdeniz Havzasi
D08A142 GERİN D. BOZALAN

YERİ: MİLAS-ÖREN-ÇÖKERIME YOLUNUN 11KM.SİNDEN SAĞA AYRILAN BOZALAN YOLUNU 1.KM.SİNDENDİR..
27°50'4" Doğu - 37°1'47" Kuzey
YAĞIŞ ALANI: 26.20 km2 YAKLAŞIK KOT: 34 m
GÖZLEM SÜRESİ: 01.10.2004 - 30.09.2006

			ÖLÇÜLEN AKIMLAR		
EŞEL SEVİYESİ (CM)	AKIM(M3/SN)	TARİH	EŞEL SEVİYESİ (CM)	AKIM(M3/SN)	TARİH
20	0,011	23.01.2006	26	0,145	10.02.2006

09. Antalya Havzasi
D09G009 EGRİDİR G. GÖL GÖZLEM

YERİ: EGİRDİR İLÇESİNDEKİ KALEBURUN MEVKİİNDEDİR.
30°49'47" Doğu-37°52'42" Kuzey
YAĞIŞ ALANI: 3321.00 km2 YAKLAŞIK KOT: 914.62 m
GÖZLEM SÜRESİ: 01.05.1958 - 30.09.2006

09. Antalya Havzasi
D09G017 KOVADA G. GÖL GÖZLEM

YERİ: EGİRDİR-KEPEZ HİDROELEKTİRİK SANTRALI YOLUNUN 29. KM SİNDEKİ KOVADA GÖLÜ ÇIKIŞ KANALI ÖNÜNDEDİR.

30°52'0" Doğu-37°37'0" Kuzey
YAĞIŞ ALANI: 3728.00 km2 YAKLAŞIK KOT: 902.94 m
GÖZLEM SÜRESİ: 11.05.1961 - 30.09.2006

09. Antalya Havzasi
D09G045 ONAÇ BRJ. GÖL GÖZLEM

YERİ: ISPARTA-BUCAK YOLUNU TAKİBEN BUCAK İLÇESİNE 1KM KALA SOLA SAPILARAK ONAÇ BARAJINA VARILIR. İSTASYON BARAJ GÖVDESINE KADEMELİ EŞELLİ OLARAK TESİS EDILMIŞTIR. HARİTA PAFTA NO:N25-A1
30°34'5" Doğu-37°28'54" Kuzey
YAĞIŞ ALANI: 269.20 km2 YAKLAŞIK KOT: 810 m
GÖZLEM SÜRESİ: 07.12.1966 - 30.09.2006

09. Antalya Havzasi
D09G059 HOYRAN G. GÖL GÖZLEM

YERİ: ISPARTA-BARLA KASABASI YOLUNU TAKİBEN BARLA KASABASINDAN 18 KM SONRAKİ AKKEÇİLİ KÖYÜ MEVKİİNDEDİR.
30°48'0" Doğu-38°8'0" Kuzey
YAĞIŞ ALANI: 3321.00 km2 YAKLAŞIK KOT: 914.62 m
GÖZLEM SÜRESİ: 18.12.1972 - 30.09.2006

09. Antalya Havzasi
D09A073 PUPA Ç. SENİRKENT

YERİ: SENİRKENT BÜYÜK KABACA YOLUNU TAKİBEN YAKLAŞIK 5 KM SONRA SAĞA KANAL YOLUNA SAPILARAK 500 M. SONRA İSTASYONA VARILIR. HARİTA PAFTA NO: L25-D4
30°36'12" Doğu - 38°8'4" Kuzey
YAĞIŞ ALANI: 291.00 km2 YAKLAŞIK KOT: 935 m
GÖZLEM SÜRESİ: 01.10.1986 - 30.09.2006

09. Antalya Havzasi
D09A081 ULUBORLU BRJ. ÇIKIŞ

YERİ: ISPARTA ULUBORLU YOLUNU TAKİBEN BARAJA VARILIR. İSTASYON BARAJIN DOLUSAVAK ÇIKIŞINDADIR. HARİTA PAFTA NO:L24-C3
30°24'51" Doğu - 38°3'45" Kuzey
YAĞIŞ ALANI: 46.30 km2 YAKLAŞIK KOT: 1095 m
GÖZLEM SÜRESİ: 01.02.1984 - 30.09.2006

09. Antalya Havzasi
D09A090 SORGUN D. ANAMAS

YERİ: ISPARTA-EĞİRDİR-ANAMAS YOLUNDAN ZİNDAN BOĞAZI-SUYUN GÖZÜ 500 M SONRADA İSTASYONA VARILIR. HARİTA PAFTA NO: M26-A4
31°5'45" Doğu - 37°50'31" Kuzey
YAĞIŞ ALANI: 21.40 km2 YAKLAŞIK KOT: 1360 m
GÖZLEM SÜRESİ: 01.10.1986 - 30.09.2006

09. Antalya Havzasi
D09G096 KARACAÖREN BRJ. GÖL GÖZLEM

YERİ: ISPARTA-ANTALYA DEREBOĞAZI YOLUNA TAKİBEN KARACAÖREN BARAJ YOLUNA SAPILIR,1.5 KM SONRA BARAJ TESİSLERINE VARILIR.ORADAN 500 M SONRA BARAJ GÖVDESİNDE TESİS EDİLMİŞTİR.
30°49'54" Doğu-37°22'14" Kuzey
YAĞIŞ ALANI: 3820.00 km2 YAKLAŞIK KOT: 230 m
GÖZLEM SÜRESİ: 01.10.1989 - 30.09.2006

09. Antalya Havzasi
D09A098 AKSU Ç. KARGI REGÜLATÖRÜ

YERİ: ANTALYA AKSU YOLUNDAN GİDİLEREK KURŞUNLU ŞELALESİ YOLUNDAN DEVAM EDİLEREK YAKLAŞIK 30 KM. SONRA İSTASYONA VARILIR.(PAFTA N25 - C1)
30°48'18" Doğu - 37°16'15" Kuzey
YAĞIŞ ALANI: 5546.40 km2 YAKLAŞIK KOT: 73 m
GÖZLEM SÜRESİ: 16.12.1993 - 31.09.2006

09. Antalya Havzasi
D09G113 EGRİDİR G. GÖL GÖZLEM

YERİ: EĞİRDİR-GELENDOST YOLUNU TAKİBEN MAHMATLAR KÖYÜNDEN 2 KM SONRA BALIKÇI BARINAĞINA VARILIR. İSTASYON LİMANIN GİRİŞİNİN SOL SAHİLİNE TESİS EDİLMİŞTİR.
30°57'38" Doğu-37°58'18" Kuzey
YAĞIŞ ALANI: 3321.00 km2 YAKLAŞIK KOT: 914.62 m
GÖZLEM SÜRESİ: 01.10.1998 - 30.09.2006

10. Burdur Göller Havzasi
D10A007 DEĞİRMENLER D. KARAMANLI

YERİ: BURDUR-KARAMANLI YOLUNU TAKIBEN KARAMANLI GİRİŞİNDEN SAĞA YEŞILOVA YOLUNU TAKIBEN 3 KM. SONRA SAĞA GİRİLEREK İSTASYONA VARILIR. HARİTA PAFTA NO:N23-B1
29°50'14" Doğu - 37°23'39" Kuzey
YAĞIŞ ALANI: 171.00 km2 YAKLAŞIK KOT: 1145 m
GÖZLEM SÜRESİ: 24.04.1962 - 30.09.2006

10. Burdur Göller Havzasi
D10G008 KARATAŞ G. GÖL GÖZLEM

YERİ: BURDUR-TEFENNİ YOLUNUN 5. KM SİNDEN SOLA AYRILAN YOLUN 8. KM SİNDEKİ KARATAŞ GÖLÜNDEDİR.
29°59'0" Doğu-37°23'0" Kuzey
YAĞIŞ ALANI: 822.00 km2 YAKLAŞIK KOT: 1050 m
GÖZLEM SÜRESİ: 01.10.2000 - 30.09.2006

10. Burdur Göller Havzasi
D10G021 KARAMANLI BRJ. GÖL GÖZLEM
YERİ: TEFENNİ-YEŞİLOVA YOLUNUN 11.5 KM SİNDEKİ KARAMANLI BARAJ GÖLÜNDEDİR.
29°50'0" Doğu-37°23'0" Kuzey
YAĞIŞ ALANI: 163.40 km2 YAKLAŞIK KOT: 1164.12 m
GÖZLEM SÜRESİ: 01.03.1974 - 30.09.2006

10. Burdur Göller Havzasi
D10A034 BAYNAZ DERESİ BAYRAMLAR
YERİ: BURDUR-TEFENNİ YOLUNU TAKİBEN BAYRAMLAR YOLUNA DÖNÜLÜR. İSTASYON KÖY GİRİŞINDEKİ KÖPRÜNÜN 300 MT DERENİN MEMBASINDADIR.
29°49'34" Doğu - 37°14'7" Kuzey
YAĞIŞ ALANI: 52.00 km2 YAKLAŞIK KOT: 1206 m
GÖZLEM SÜRESİ: 01.07.2006 - 30.09.2006

11. Akarçay Havzasi
D11A001 EBER G. ÇIKIŞ
YERİ: AFYON SULTANDAĞI YOLUNU TAKİBEN SOLA SAPILARAK EBER GÖLÜNE VARILIR. İSTASYON EBER GÖLÜNÜ ÇIKIŞ KANALINDAKİ REG. DEDİR. HARİTA PAFTA NO:K26-D3
31°13'53" Doğu - 38°36'35" Kuzey
YAĞIŞ ALANI: 5288.40 km2 YAKLAŞIK KOT: 970 m
GÖZLEM SÜRESİ: 04.06.1959 - 30.09.2006

11. Akarçay Havzasi
D11G003 AKŞEHİR G. GÖL GÖZLEM
YERİ: SULTANDAĞI İLÇESİNDEN ÇIKILIR. TAŞKÖPRÜ KÖYÜNE VARILIR. KÖYDEKİ BALIK HANELERİN YANINDADIR. HARİTA PAFTA NO: K26.C4
31°17'23" Doğu-38°34'47" Kuzey
YAĞIŞ ALANI: 7963.00 km2 YAKLAŞIK KOT: 954 m
GÖZLEM SÜRESİ: 26.08.1961 - 30.09.2006

11. Akarçay Havzasi
D11G004 EBER G. GÖL GÖZLEM
YERİ: ÇAY-AKŞEHİR YOLUNU TAKİBEN YAKASENEK KAVŞAĞINDAN SOLA DÖNÜLEREK YAKLAŞIM KANALINA VARILIR.YAKLAŞIM KANALI İLE EBER GÖLÜNÜN BİRLEŞTİĞİ YERDE OLUP ELEKTRONİK LİMNİGRAFLIDIR.
31°10'55" Doğu-38°37'7" Kuzey
YAĞIŞ ALANI: 5005.00 km2 YAKLAŞIK KOT: 964 m
GÖZLEM SÜRESİ: 05.10.1961 - 30.09.2006

11. Akarçay Havzasi
D11G005 SEYİTLER BRJ. GÖL GÖZLEM
YERİ: AFYONDAN ANKARA YOLU TAKİBEN GEBECELER KASABASINA SAĞA DÖNÜLÜR. GEBECELERDEN 3 KM MESAFEDEKİ SEYİTLER BARAJINA GEÇİLİR. BARAJ GÖVDESİNİN SAĞ TARAFINDA OLUP KADEMELİ EŞELLİDİR.
30°47'9" Doğu-38°47'29" Kuzey
YAĞIŞ ALANI: 306.40 km2 YAKLAŞIK KOT: 1034 m
GÖZLEM SÜRESİ: 27.12.1962 - 30.09.2006

11. Akarçay Havzasi
D11A006 SEYİTLER BRJ. ÇIKIŞ
YERİ: SEYİTLER BARAJI DİPSAVAK ÇIKIŞININ 250 M MANSABINDADIR
30°47'13" Doğu - 38°47'7" Kuzey
YAĞIŞ ALANI: 296.00 km2 YAKLAŞIK KOT: 1017 m
GÖZLEM SÜRESİ: 11.03.1963 - 30.09.2006

11. Akarçay Havzasi
D11G009 SELEVİR BRJ. GÖL GÖZLEM
YERİ: AFYON-ÇAY YOLUNU TAKİBEN DİNAR YOL AYRIMINA DÖNÜLÜR 4 KM SONRA KARACAÖREN KASABASINDAN SAĞA SAPILARAK İNLİ KÖYÜ YOLUNA GİRİLİR. KÖYÜ GEÇTİKTEN SONRA BARAJA VARILIR. İSTASYON BARAJ GÖVDESİNDEDİR. HARİTA PAFTA NO: K25-D3
30°43'4" Doğu-38°30'46" Kuzey
YAĞIŞ ALANI: 742.00 km2 YAKLAŞIK KOT: 1073 m

11. Akarçay Havzasi
D11G011 KARAMIK G. GÖL GÖZLEM
YERİ: ÇAY - KARADİLLİ YOLUNUN 18. KM SİNDEKİ AKKONAK BELDESİNDEN SOLA AYRILAN YOLUN 14 KM SİNDEKİ KOÇBEYLİ KSB. GEÇİLEREK SU BATANA VARILIR. BÜYÜK DÜDENİN 100 M YAKININDADIR.
30°51'47" Doğu-38°24'45" Kuzey
YAĞIŞ ALANI: 342.00 km2 YAKLAŞIK KOT: 1000 m
GÖZLEM SÜRESİ: 28.01.1965 - 30.09.2006

11. Akarçay Havzasi
D11A012 SELEVİR BRJ. ÇIKIŞ
YERİ: AFYON-ÇAY KARAYOLU DİNAR KAVŞAĞINDAN SAĞA DÖNÜLEREK KARACAÖREN 'DEN SAĞA INLI KASABASINA GEÇILİR SELEVIR BARAJINA VARMADAN DIPSAVAK ÇIKIŞININ 1 KM AŞAĞISINDADIR. HARİTA PAFTA NO: K25-C4
30°44'14" Doğu - 38°31'45" Kuzey
YAĞIŞ ALANI: 742.00 km2 YAKLAŞIK KOT: 1060 m
GÖZLEM SÜRESİ: 01.04.1965 - 30.09.2006

11. Akarçay Havzasi
D11A024 KURUÇAY D. SİNCANLI
YERİ: AFYON-SANDIKLI YOLUNU TAKİBEN SINANPAŞA İLÇESİNE VARIRKEN ESKİ TIFTIK FABRIKASI YANINDAN SOLA DÖNÜLEREK KURUÇAY DERESINE VARILIR. İSTASYON DERE ÜZERİNDE SAĞ SAHİLDEDİR. HARİTA PAFTA NO: K24-D2
30°14'31" Doğu - 38°42'33" Kuzey

YAĞIŞ ALANI: 22.69 km2 YAKLAŞIK KOT: 1170 m
GÖZLEM SÜRESİ: 14.08.1997 - 30.09.2006

12. Sakarya Havzasi
D12G004 PORSUK BRJ. GÖL GÖZLEM

YERİ: 30°16'0" Doğu-39°38'0" Kuzey
YAĞIŞ ALANI: ---- km2 YAKLAŞIK KOT: 862 m
GÖZLEM SÜRESİ: 01.03.1956 - 30.09.2006(30 Yıl)

12. Sakarya Havzasi
D12G010 ÇUBUK- 1 BARAJI GÖL GÖZLEM

YERİ: ANKARA-ÇUBUK-I BARAJI KRETİN ÖN KISMINDA YER ALMAKTADIR.
32°56'0" Doğu-40°0'18" Kuzey
YAĞIŞ ALANI: 1020.00 km2 YAKLAŞIK KOT: 885 m
GÖZLEM SÜRESİ: 01.01.1954 - 30.09.2006(49 Yıl)

12. Sakarya Havzasi
D12A034 PORSUK Ç. PORSUK BARAJİ ÇIKIŞ

YERİ: ESKİŞEHİRE 42 KM MESAFEDEKİ PORSUK BARAJ AKSININ 1 5 KMMANSABINDADIR. LİMNIGRAFLI
30°16'47" Doğu - 39°38'5" Kuzey
YAĞIŞ ALANI: 465.50 km2 YAKLAŞIK KOT: 842 m
GÖZLEM SÜRESİ: 01.10.1962 - 30.09.2006

			ÖLÇÜLEN AKIMLAR		
EŞEL SEVİYESİ (CM)	AKIM(M3/SN)	TARİH	EŞEL SEVİYESİ (CM)	AKIM(M3/SN)	TARİH
39	2.768	03.10.2005	98	17.903	31.05.2006
38	1.811	09.11.2005	95	15.477	12.07.2006
39	1.726	09.03.2006	77	12.869	01.09.2006
40	1.203	06.04.2006	40	1.832	28.09.2006

12. Sakarya Havzasi
D12G096 KAYAŞ BAYINDIR BARAJI GÖL GÖZLEM

YERİ: ANKARA KAYAŞ YOLU ÜZERİNDE BAYINDIR BARAJI GÖVDESİNDE KADEMELİ OLARAK TESİS EDİLMİŞTİR.
33°0'0" Doğu-39°55'0" Kuzey
YAĞIŞ ALANI: 69.40 km2 YAKLAŞIK KOT: 972 m
GÖZLEM SÜRESİ: 01.10.1968 - 30.09.2006(35 Yıl)

12. Sakarya Havzasi
D12G097 ÇUBUK-2 BARAJI GÖL GÖZLEM

YERİ: ANKARA ÇUBUK İLÇESİNDEN KARAGÖL YOLUNA SAPILIR.3 KM. SONRA AŞAĞI ÇAVUNDUR KÖYÜNE,ORADAN DA.2 KM. SONRA BARAJA VARILIR. İSTASYON GÖVDE ÖNÜNDE KADEMELİ OLARAK TESİS EDİLMİŞTİR.
33°1'0" Doğu-40°17'0" Kuzey
YAĞIŞ ALANI: 180.00 km2 YAKLAŞIK KOT: 1100 m
GÖZLEM SÜRESİ: 01.10.1966 - 30.09.2006(28 Yıl)

12. Sakarya Havzasi
D12A099 SEY DERESİ GÜVEM

YERİ: KIZILCAHAMAM-GÜVEM YOLUNDA, GÜVEM JANDARMA KARAKOLUNUN ARKASINDA SAĞ SAHİLDEDİR.
32°39'31" Doğu - 40°35'32" Kuzey
YAĞIŞ ALANI: 205.20 km2 YAKLAŞIK KOT: 1081 m
GÖZLEM SÜRESİ: 31.01.1967 - 30.09.2006

12. Sakarya Havzasi
D12A101 KARGİN D. REG.DERİVASYON KAN.

YERİ: ESKİŞEHİRE 39 KM DEKİ PORSUK BRJ-SABUNCUPINAR BUCAĞI YOLU-NUN 6.KMDEKİ KARGIN REGÜLATÖR ÇIKIŞINDADIR.EŞELLİ.
30°16'0" Doğu - 39°36'0" Kuzey
YAĞIŞ ALANI: 317.30 km2 YAKLAŞIK KOT: 896 m
GÖZLEM SÜRESİ: 01.10.1970 - 30.09.2006

			ÖLÇÜLEN AKIMLAR		
EŞEL SEVİYESİ (CM)	AKIM(M3/SN)	TARİH	EŞEL SEVİYESİ (CM)	AKIM(M3/SN)	TARİH
2	0.021	09.11.2005	9	0.398	09.05.2006
24	2.159	09.03.2006	4	0.075	16.06.2006
5	0.109	31.05.2006	3	0.025	12.07.2006

12. Sakarya Havzasi
D12G102 Kargin G. Göl Gözlem

YERİ: 30°16'0" Doğu-39°36'0" Kuzey
YAĞIŞ ALANI: ---- km2 YAKLAŞIK KOT: 898 m

12. Sakarya Havzasi
D12A103 HIZARLI D. KARGİN REG. GİRİŞ

YERİ: ESKİŞEHİRE 39. KM MESAFEDEKİ PORSUK BARAJI SABUNCUPINAR BUCAĞI YOLUNUN 6 KM SİNDEKİ REGÜLATÖR GİRİŞİNDEDİR.
30°16'0" Doğu - 39°35'0" Kuzey

YAĞIŞ ALANI: 84.40 km2 YAKLAŞIK KOT: 900 m
GÖZLEM SÜRESİ: 08.01.1969 - 30.09.2006

12. Sakarya Havzasi
D12G122 KURTBOĞAZI BARAJI GÖL GÖZLEM

YERİ: ANKARA-KIZILCAHAMAM YOLUNUN 50 KM.'SİNDEN, KAZAN İLÇESİNİ GEÇİNCE KURTBOĞAZI BARAJINA VARILIR.İSTASYON KADEMELİ OLARAK GÖVDEYE TESİS EDİLMİŞTİR.
32°41'0" Doğu-40°16'0" Kuzey
YAĞIŞ ALANI: 336.70 km2 YAKLAŞIK KOT: 912 m
GÖZLEM SÜRESİ: 01.10.1976 - 30.09.2006(35 Yıl)

12. Sakarya Havzasi
D12G133 SAPANCA G. GÖL GÖZLEM

YERİ: E5 KARAYOLU YANI SASKİ TESİSLERİ.
30°17'36" Doğu-40°44'16" Kuzey
YAĞIŞ ALANI: ---- km2 YAKLAŞIK KOT: 31 m
GÖZLEM SÜRESİ: 01.05.1975 - 30.09.2006(17 Yıl)

12. Sakarya Havzasi
D12G145 Dodurga Brj. Göl Gzlem

YERİ: 29°57'0" Doğu-39°47'0" Kuzey
YAĞIŞ ALANI: ---- km2 YAKLAŞIK KOT: 1038 m
GÖZLEM SÜRESİ: 01.10.1977 - 30.09.2006(25 Yıl)

12. Sakarya Havzasi
D12A149 DODURGA BRJ. ÇIKIŞ

YERİ: ESKİŞEHİR BOZUYÜK İLÇESİ 20.KM DEKİ DODURGA BARAJININ 100 MTMANSABINDADIR.EŞELDEN DEĞERLENDİRİLDİ.
29°57'0" Doğu - 39°47'0" Kuzey
YAĞIŞ ALANI: 182.00 km2 YAKLAŞIK KOT: 1034 m
GÖZLEM SÜRESİ: 01.11.1980 - 30.09.2006

ÖLÇÜLEN AKIMLAR

EŞEL SEVİYESİ (CM)	AKIM(M3/SN)	TARİH	EŞEL SEVİYESİ (CM)	AKIM(M3/SN)	TARİH
23	1.172	13.06.2006	24	1.214	14.07.2006

12. Sakarya Havzasi
D12A156 BEDRESU ISAÖREN

YERİ: BURSA-İNEGÖL KAZASININ İSAÖREN KÖYÜ İÇİNDEN GEÇEN DERE NİNSOL SAHİLİNDEKİ DUVARDADIR.
29°30'0" Doğu - 40°2'0" Kuzey
YAĞIŞ ALANI: 59.12 km2 YAKLAŞIK KOT: 325 m
GÖZLEM SÜRESİ: 23.12.1980 - 30.09.2006

12. Sakarya Havzasi
D12G162 Kaymaz Brj. Göl Gözlem

YERİ: 31°13'0" Doğu-39°32'0" Kuzey
YAĞIŞ ALANI: ---- km2 YAKLAŞIK KOT: 1040 m

12. Sakarya Havzasi
D12G169 Sögüt Brj. Göl Gözlem

YERİ: 30°11'0" Doğu-39°26'0" Kuzey
YAĞIŞ ALANI: ---- km2 YAKLAŞIK KOT: 1113 m

12. Sakarya Havzasi
D12A173 PORSUK Ç. GÖKÇEKIŞIK

YERİ: ESKİŞEHİR KÜTAHYA YOLUNUN 8.KMSİNDEN SOLA AYRILAN YOLUN13.KMDEKİ GÖKÇEKISIK KÖYÜNDEDİR
30°24'0" Doğu - 39°39'0" Kuzey
YAĞIŞ ALANI: 5425.00 km2 YAKLAŞIK KOT: 832 m
GÖZLEM SÜRESİ: 01.10.1983 - 30.09.2005

ÖLÇÜLEN AKIMLAR

EŞEL SEVİYESİ (CM)	AKIM(M3/SN)	TARİH	EŞEL SEVİYESİ (CM)	AKIM(M3/SN)	TARİH
30	2.820	03.10.2005	25	2.412	07.04.2006
27	2.304	08.11.2005	93	16.738	31.05.2006
25	2.429	09.12.2005	85	13.026	15.06.2006
38	5.305	14.03.2006	80	12.413	10.07.2006
25	2.483	06.04.2006	77	12.433	01.08.2006

12. Sakarya Havzasi
D12A178 HOCAKÖY D. ÇİFTELER

YERİ: ESKİŞEHİR ÇİFTELER KAZASINA 40 KM MESAFEDEKİ HAN KÖYE 2 KM UZAKLIKTADIR.
30°62'0" Doğu - 39°8'0" Kuzey
YAĞIŞ ALANI: 54.85 km2 YAKLAŞIK KOT: 1180 m
GÖZLEM SÜRESİ: 01.10.1984 - 30.09.2006

12. Sakarya Havzasi
D12G179 KUNDUZLAR BRJ. GÖL GÖZLEM

YERİ: 30°35'0" Doğu-39°21'0" Kuzey

YAĞIŞ ALANI: 406.00 km2 YAKLAŞIK KOT: 1010.91 m
GÖZLEM SÜRESİ: 01.10.1984 - 30.11.2006(19 Yıl)

12. Sakarya Havzasi
D12A183 KEÇELİÖZÜ D. GÖKNEBİ

YERİ: ESKİŞEHİR-SEYİTGAZİ İLÇESİNE 18 KM MESAFEDEKİ GÖKNEBİKÖYÜNE 5 KM MESAFEDEDİR.
30°31'0" Doğu - 39°22'0" Kuzey
YAĞIŞ ALANI: 94.85 km2 YAKLAŞIK KOT: 2032 m
GÖZLEM SÜRESİ: 01.10.1985 - 30.09.2006

			ÖLÇÜLEN AKIMLAR		
EŞEL SEVİYESİ (CM)	AKIM(M3/SN)	TARİH	EŞEL SEVİYESİ (CM)	AKIM(M3/SN)	TARİH
3	0.146	19.04.2006	4	0.048	26.05.2006

12. Sakarya Havzasi
D12G187 ÇAMLIDERE BARAJI GÖL GÖZLEM

YERİ: KIZILCAHAMAM YOLU ÜZERİNDEN KIZILCAHAMAM'A 1 KM. KALA ÇELTIKÇI YOLUNA SAPILIR.İLERİDE ÇELTİKÇİ'YE GİRMEDEN ÇAMLIDERE BARAJINA GİDEN YOLA SAPILIR. 27 KM. SONRA ÇAMLIDERE BARAJINA VARILIR.
32°24'0" Doğu-40°23'0" Kuzey
YAĞIŞ ALANI: 753.00 km2 YAKLAŞIK KOT: 912 m
GÖZLEM SÜRESİ: 01.11.1985 - 30.09.2006(20 Yıl)

12. Sakarya Havzasi
D12G195 Çatören Brj. Göl Gözlem

YERİ: 30°34'0" Doğu-39°19'0" Kuzey
YAĞIŞ ALANI: ---- km2 YAKLAŞIK KOT: 1015 m
GÖZLEM SÜRESİ: 01.12.1987 - 30.09.2006(16 Yıl)

12. Sakarya Havzasi
D12A198 YİRMAÇ D. İNEKÇİKÖY

YERİ: ADAPAZARI KAYNARCA 33.KM ASFALT KAYNARCA-İSTASYON 12.KMSTABİLİZE
30°25'41" Doğu - 41°5'18" Kuzey
YAĞIŞ ALANI: 284.74 km2 YAKLAŞIK KOT: 16.2490 m
GÖZLEM SÜRESİ: 14.12.1988 - 30.09.2006

			ÖLÇÜLEN AKIMLAR		
EŞEL SEVİYESİ (CM)	AKIM(M3/SN)	TARİH	EŞEL SEVİYESİ (CM)	AKIM(M3/SN)	TARİH
54	3.309	13.12.2005	71	7.919	27.02.2006
54	3.256	18.01.2006	33	1.058	12.04.2006

12. Sakarya Havzasi
D12G202 SAPANCA GÖLÜ SAPANCA GÖLÜ UZUNKUM

YERİ: 30°18'08" Doğu-40°41'57" Kuzey
YAĞIŞ ALANI: 249.00 km2 YAKLAŞIK KOT: 29.46 m
GÖZLEM SÜRESİ: 07.11.1989 - 30.09.2006(17 Yıl)

12. Sakarya Havzasi
D12A206 SABUNCU D. KURTKÖY

YERİ: ESKİŞEHİRDEN 45 KM SONRA BOZÜYÜKE VARILIP ARADAN 15 KMSİNDEDEMİRKÖYE DEMİRKÖYDEN 4 KM SONRA KURTKÖY,E VARILIR.KÖYÜN
30°4'2" Doğu - 39°59'22" Kuzey
YAĞIŞ ALANI: 26.20 km2 YAKLAŞIK KOT: 735 m
GÖZLEM SÜRESİ: 01.10.1989 - 30.09.2006

12. Sakarya Havzasi
D12A209 DEDEBAĞ D. NASRETTİN HOCA

YERİ: ESKİŞEHİRDEN SİVRİHİSARA VARILIR.ANKARA YOLUNUN 110 KMSİNDEN SAĞDA NASREDDİN HOCA KÖYÜNE VARILIR.İSTASYON 2 KM MESAFEDEDİR
31°40'0" Doğu - 39°30'0" Kuzey
YAĞIŞ ALANI: 25.45 km2 YAKLAŞIK KOT: 900 m
GÖZLEM SÜRESİ: 15.12.1993 - 30.09.2006

			ÖLÇÜLEN AKIMLAR		
EŞEL SEVİYESİ (CM)	AKIM(M3/SN)	TARİH	EŞEL SEVİYESİ (CM)	AKIM(M3/SN)	TARİH
4	0.215	17.11.2005	4	0.161	20.01.2006
4	0.158	19.01.2006	8	0.173	14.06.2006

12. Sakarya Havzasi
D12A210 AKÇAY D. DOGANCİLAR

YERİ: ESKISEHIR-ISTANBUL YOLUNDAN BILECIK E VRILIR. VEZIRHAN-GOLPAZARI-TARAKLI YOLUNUN 6. KM SINDEN SAPILIR VE 3 KM SONRA
30°24'0" Doğu - 40°17'0" Kuzey
YAĞIŞ ALANI: 35.00 km2 YAKLAŞIK KOT: 650 m
GÖZLEM SÜRESİ: 01.10.1993 - 30.09.2006

			ÖLÇÜLEN AKIMLAR		
EŞEL SEVİYESİ (CM)	AKIM(M3/SN)	TARİH	EŞEL SEVİYESİ (CM)	AKIM(M3/SN)	TARİH
1	0.030	07.10.2005	10	0.838	13.03.2006
3	0.022	10.11.2005	6	0.224	14.04.2006
8	0.190	20.01.2006	5	0.138	04.05.2006

12. Sakarya Havzasi
D12A215 PORSUK Ç. PARSİBEY

YERİ: ESKİŞEHİR ANKARA YOLUNUN 55. SOLA DÖNÜLÜR.20 KM SONRA BEYLİK OVAYA VARILIR.5 KM SONR PARSİBEYDEKI AKIIM IST. ULAŞILIR
31°9'39" Doğu - 39°41'19" Kuzey
YAĞIŞ ALANI: 8671.00 km2 YAKLAŞIK KOT: 750 m
GÖZLEM SÜRESİ: 07.09.1994 - 30.09.2006

			ÖLÇÜLEN AKIMLAR		
EŞEL SEVİYESİ (CM)	AKIM(M3/SN)	TARİH	EŞEL SEVİYESİ (CM)	AKIM(M3/SN)	TARİH
72	1.084	26.12.2005	84	7.049	13.04.2006
120	6.304	23.02.2006	125	7.638	18.05.2006

12. Sakarya Havzasi
D12A220 KEMALİYE DEĞİRMENDERE

YERİ: SAKARYA-PAMUKOVA İLÇESİ KEMALİYE KÖYÜNDEDİR.
30°0'0" Doğu - 40°31'0" Kuzey
YAĞIŞ ALANI: 22.50 km2 YAKLAŞIK KOT: 725 m
GÖZLEM SÜRESİ: 01.10.1996 - 30.09.2006

12. Sakarya Havzasi
D12G222 EĞREKKAYA BARAJI GÖL GÖZLEM

YERİ: ANKARA-KIZILCAHAMAM İLÇESİNE 1,5 KM. MESAFEDE ESKİ ÇERKEŞ YOLU ÜZERİNDEDİR.
32°38'60" Doğu-40°29'33" Kuzey
YAĞIŞ ALANI: 410.00 km2 YAKLAŞIK KOT: 973 m
GÖZLEM SÜRESİ: 01.11.1992 - 30.09.2006(5 Yıl)

12. Sakarya Havzasi
D12A223 ANKARA Ç. SARIOBA KÖPRÜSÜ

YERİ: ANKARA AYAŞ İLÇESİNİN 1 KM ALTINDA POLATLIYA AYRILAN YOLUN 35.KM SİNDE SARIOBA BELDESİNİN İÇİNDE ANKARA ÇAYI ÜZERİNDEKİ KÖYÜN KÖPRÜSÜNÜN 150 M.MANSABINDADIR.
32°5'0" Doğu - 39°51'50" Kuzey
YAĞIŞ ALANI: 6890.00 km2 YAKLAŞIK KOT: 667 m
GÖZLEM SÜRESİ: 13.08.1997 - 30.09.2006

12. Sakarya Havzasi
D12A229 ULUDERE KARAPÜRÇEK

YERİ: ADAPAZARI KARAPÜRÇEK KÖYÜNDEDİR.
30°31'0" Doğu - 40°37'0" Kuzey
YAĞIŞ ALANI: 24.14 km2 YAKLAŞIK KOT: 185 m
GÖZLEM SÜRESİ: 01.10.1997 - 30.09.2006

12. Sakarya Havzasi
D12A231 KOCADERE FETHİYE

YERİ: BURSA YENİŞEHİR KARA YOLU ÜZERİNDE BULUNAN KOYUNHİSARDANSOLA SAPILARAK 6KM SONRA FETHİYE KÖYÜNE VARILIR.İSTASYON
40°17'51" Doğu - 29°27'16" Kuzey
YAĞIŞ ALANI: 85.70 km2 YAKLAŞIK KOT: 3030 m
GÖZLEM SÜRESİ: 01.10.1998 - 30.09.2006

12. Sakarya Havzasi
D12A234 MEŞELİ D. BEŞEVLER

YERİ: ADAPAZARI -MAHMUDİYE YOLUNUN 18. KM.dedir.
31°1'0" Doğu - 39°44'0" Kuzey
YAĞIŞ ALANI: 970.00 km2 YAKLAŞIK KOT: 54 m
GÖZLEM SÜRESİ: 22.09.2000 - 30.09.2006

			ÖLÇÜLEN AKIMLAR		
EŞEL SEVİYESİ (CM)	AKIM(M3/SN)	TARİH	EŞEL SEVİYESİ (CM)	AKIM(M3/SN)	TARİH
26	0.043	11.11.2005	46	0.884	08.03.2006
34	0.480	31.01.2006	28	0.037	09.05.2006
45	0.846	10.02.2006	27	0.034	14.06.2006

12. Sakarya Havzasi
D12A236 GÖLCÜK D. BEYAZALTIN

YERİ: ESKİŞEHİR-MERKEZ SEPETÇİ KÖYÜNDEDİR.
30°50'0" Doğu - 39°55'0" Kuzey
YAĞIŞ ALANI: 5.90 km2 YAKLAŞIK KOT: 930 m
GÖZLEM SÜRESİ: 06.09.2000 - 30.09.2006

			ÖLÇÜLEN AKIMLAR		
EŞEL SEVİYESİ (CM)	AKIM(M3/SN)	TARİH	EŞEL SEVİYESİ (CM)	AKIM(M3/SN)	TARİH
4	0.016	16.12.2005	5	0.059	07.04.2006
2	0.015	26.12.2005	4	0.022	13.04.2006
10	0.327	23.02.2006	2	0.009	18.05.2006

12. Sakarya Havzasi
D12G239 AKYAR BARAJI GÖL GÖZLEM
YERİ: ANKARA-İSTANBUL KARAYOLUNUN 100. KM' SİNDE AZAPHANE DERESİNE GİRMEDEN BULAK KÖYÜNE DÖNÜLÜR.BARAJ,KÖYE 2 KM. MESAFEDEDİR.
32°34'47" Doğu-40°34'60" Kuzey
YAĞIŞ ALANI: 253.00 km2 YAKLAŞIK KOT: 1065 m
GÖZLEM SÜRESİ: 25.12.2000 - 30.09.2006(4 Yıl)

12. Sakarya Havzasi
D12G241 ASARTEPE BARAJI GÖL GÖZLEM
YERİ: ANKARA-AYAŞ KARAYOLU 34 KM. SİNDE, SAĞA ORTABEREKET KÖYÜNE DÖNÜLÜR.4 KM. SONRA ORTABEREKET KÖYÜNE VARILIR.ASARTEPE BARAJI ORTABEREKET KÖYÜNE TAKRİBEN 7 KM. MESAFEDEDİR.
32°23'15" Doğu-40°8'45" Kuzey
YAĞIŞ ALANI: 239.00 km2 YAKLAŞIK KOT: 881 m
GÖZLEM SÜRESİ: 01.10.2000 - 30.09.2006(4 Yıl)

13. Bati Karadeniz Havzasi
D13G001 EFTENİ GÖLÜ GÖL GÖZLEM
YERİ: ÇINARLI -GÖLYAKA YOLU GÖL ORMANINDAN 2 KM. SONRA YOLUN SAĞINDADIR.
31°3'0" Doğu-40°45'0" Kuzey
YAĞIŞ ALANI: 1860.00 km2 YAKLAŞIK KOT: 1 m
GÖZLEM SÜRESİ: 11.10.1960 - 30.09.2006(37 Yıl)

13. Bati Karadeniz Havzasi
D13A014 ULUS Ç. BAYIRYÜZÜ
YERİ: BARTIN SAFRANBOLU KARAYOLUNUN 21.KM SİNDEKİ KİRAZLIK KÖPRÜNÜN 150 M. MANSABINDADIR.
32°24'41" Doğu - 41°33'37" Kuzey
YAĞIŞ ALANI: 1016.00 km2 YAKLAŞIK KOT: 54 m
GÖZLEM SÜRESİ: 12.04.1964 - 30.09.2006

13. Bati Karadeniz Havzasi
D13G027 GÖLKÖY BARAJI GÖL GÖZLEM
YERİ: ANKARA İSTANBUL KARAYOLU 196. KM 'DEN SOLA DÖNÜLÜR. DSİ GÖLKÖY EĞİTİM TESİSLERİNE DÖNÜLEREK TAKRİBEN 4 KM. SONRA GÖLKÖY BARAJ GÖLÜNE VARILIR.
31°31'50" Doğu-40°42'35" Kuzey
YAĞIŞ ALANI: 1205.00 km2 YAKLAŞIK KOT: 758 m
GÖZLEM SÜRESİ: 20.11.1968 - 30.09.2006(2 Yıl)

13. Bati Karadeniz Havzasi
D13G028 YENİÇAĞA GÖLÜ GÖL GÖZLEM
YERİ: ANKARA-GEREDE-BOLU YOLU ÜZERİNDE YENİÇAĞA İLÇESİNİN KENARINDAKİ YENİÇAĞA GÖLÜNÜN ÇIKIŞ TARAFINDADIR.
32°2'0" Doğu-40°46'0" Kuzey
YAĞIŞ ALANI: 147.40 km2 YAKLAŞIK KOT: 989 m
GÖZLEM SÜRESİ: 15.07.1970 - 30.09.2006(22 Yıl)

13. Bati Karadeniz Havzasi
D13G034 HASANLAR BARAJI GÖL GÖZLEM
YERİ: DÜZCE İLİ YIĞILCA İLÇESİ YOLUNUN 20.KM'SİNDE HASANLAR KÖYÜNDEDİR.
31°16'0" Doğu-40°45'0" Kuzey
YAĞIŞ ALANI: 688.40 km2 YAKLAŞIK KOT: 232 m
GÖZLEM SÜRESİ: 01.10.1975 - 30.09.2006(25 Yıl)

13. Bati Karadeniz Havzasi
D13A035 KÜÇÜK MELEN DERESİ HASANLAR BARAJI ÇIKIŞI
YERİ: DÜZCE-YIĞILCA YOLUNUN 20.KM SİNDEKİ HASANLAR BARAJININ ÇIKIŞINDAKİ KÖPRÜNÜN MENBASINDADIR.
31°16'16" Doğu - 40°54'56" Kuzey
YAĞIŞ ALANI: 618.00 km2 YAKLAŞIK KOT: 650 m
GÖZLEM SÜRESİ: 01.05.1963 - 30.09.2006

13. Bati Karadeniz Havzasi
D13A066 ASAR S. KAYNAŞLI
YERİ: KAYNAŞLI-SARIÇÖKEK KÖY YOLU 600 M. DEKİ KÖPRÜNÜN MENBASINDADIR.
31°19'16" Doğu - 40°46'48" Kuzey
YAĞIŞ ALANI: 84.00 km2 YAKLAŞIK KOT: 295 m
GÖZLEM SÜRESİ: 31.07.2002 - 30.09.2006

13. Bati Karadeniz Havzasi
D13A067 Devrek Ç. Köprübasi
YERİ: GÖKÇESU AKÇABEY YOLUNDA KÖPRÜBAŞI KÖYÜ GİRİŞİNDEDİR.
31°53'39" Doğu - 41°0'0" Kuzey
YAĞIŞ ALANI: 1998.0 km2 YAKLAŞIK KOT: 337 m
GÖZLEM SÜRESİ: 31.07.2002 - 30.09.2006

14. Yesilirmak Havzasi
D14G006 LADİK G. GÖL GÖZLEM
YERİ: LADİK REGÜLATÖRÜNÜN 10 M MENBAINDADIR. 25 LİK PAFTADAKİ YERİ: G36-A1
36°1'13" Doğu-40°55'9" Kuzey
YAĞIŞ ALANI: 145.10 km2 YAKLAŞIK KOT: 861 m
GÖZLEM SÜRESİ: 01.07.1959 - 30.09.2006

14. Yesilirmak Havzasi
D14A011 LADİK G. REG. ÇIKIŞI
YERİ: LADİK-ERBAA YOLUNUN 5 KM İLERİSİNDEKİ AŞAĞI İNÖZ KÖYÜNDEN SOLA AYRILAN YOL ÜZERİNDEKİ REGÜLATÖRÜN MANSABINDADIR.

25 LİK PAFTADAKİ YERİ: G36-A1
36°1'14" Doğu - 40°55'13" Kuzey
YAĞIŞ ALANI: 145.10 km2 YAKLAŞIK KOT: 862 m
GÖZLEM SÜRESİ: 01.05.1960 - 30.09.2006

			ÖLÇÜLEN AKIMLAR		
EŞEL SEVİYESİ (CM)	AKIM(M3/SN)	TARİH	EŞEL SEVİYESİ (CM)	AKIM(M3/SN)	TARİH
16	0,456	06.10.2005	17	0,888	13.06.2006
11	0,544	31.01.2006	16	0,811	05.07.2006
13	0,389	09.03.2006	13	0,545	10.08.2006
14	0,689	27.03.2006	12	0,352	21.09.2006
30	3,092	02.05.2006	14	0,456	06.10.2005
14	0,789	22.05.2006	15	0,482	01.11.2005

14. Yesilirmak Havzasi
D14A075 SÖĞÜTÖZÜ D. BÜYÜK SÖĞÜTÖZÜ

YERİ: ÇORUM-ALACA İLÇESİNE 8 KM. MESAFEDEKİ, ALACA BARAJININ 200 M. MANSABINDAKİ SÖĞÜTÖZÜ KÖYÜNÜN İÇİNDEDİR.
40°7'0" Doğu - 34°50'0" Kuzey
YAĞIŞ ALANI: 100.40 km2 YAKLAŞIK KOT: 1149 m
GÖZLEM SÜRESİ: 13.06.1968 - 30.09.2006

14. Yesilirmak Havzasi
D14A109 SADAK D. ÇAKIRLAR

YERİ: TRABZON ERZİNCAN YOLU ÜZERİNDE KELKİT KAZASININ İÇİNDEN SOLA AYRILAN YOLDAN ÇAKIRLAR KÖYÜNE VARILIR. İSTASYON SAĞ SAHİLDEDİR.
39°34'30" Doğu - 40°5'0" Kuzey
YAĞIŞ ALANI: 348.85 km2 YAKLAŞIK KOT: 1550 m
GÖZLEM SÜRESİ: 01.10.1984 - 30.09.2006

14. Yesilirmak Havzasi
D14G110 ALACA BARAJI GÖL GÖZLEM

YERİ: ANKARA-ÇORUM KARAYOLUNDAN ÇORUM'A GELMEDEN SAĞA ALACA İLÇESİ YOLUNA DÖNÜLEREK ALACAMERKEZİNDEN TEKRAR SAĞA DÖNÜLÜR VE BARAJ 9.KM İLERİDEKİ SÖĞÜTÖZÜ KÖYÜNDEDİR.
34°50'21" Doğu-40°6'38" Kuzey
YAĞIŞ ALANI: 91.00 km2 YAKLAŞIK KOT: 1001 m
GÖZLEM SÜRESİ: 01.08.1984 - 30.09.2006(12 Yıl)

14. Yesilirmak Havzasi
D14G115 ÇORUM BARAJI GÖL GÖZLEM

YERİ: ÇORUM'DAN SAMSUN YOLUNA GİRİLDİKTEN 3,5 KM SONRA ÇİMENTO FABRİKASINA VARILIR.ÇİMENTO FABRİKASINI 1 KM. GEÇTİKTEN SONRA SOLA DÖNÜLÜR.BARAJ 2 KM. İLERİDEDİR.
34°59'16" Doğu-40°34'58" Kuzey
YAĞIŞ ALANI: 51.5 km2 YAKLAŞIK KOT: 901 m
GÖZLEM SÜRESİ: 12.01.1982 - 30.09.2006(15 Yıl)

14. Yesilirmak Havzasi
D14A130 KÖROĞLU DERE REFAHİYE

YERİ: ERZİNCAN İLİ REFAHİYE İLÇESİNDEDİR.
38°45'59" Doğu - 39°54'44" Kuzey
YAĞIŞ ALANI: 311.00 km2 YAKLAŞIK KOT: 1564 m
GÖZLEM SÜRESİ: 01.10.1991 - 30.09.2006

14. Yesilirmak Havzasi
D14A131 ILGAR D. REFAHİYE

YERİ: ERZİNCAN İLİ REFAHİYE İLÇESİNDEDİR.
38°46'7" Doğu - 39°54'37" Kuzey
YAĞIŞ ALANI: 211.60 km2 YAKLAŞIK KOT: 1565 m
GÖZLEM SÜRESİ: 01.10.1991 - 30.09.2006

14. Yesilirmak Havzasi
D14A141 BEYLİK D. YEŞİLÖZ

YERİ: AMASYA-TURHAL KARAYOLUNUN 48 KM YEŞİLÖZ KÖYÜNÜN AŞAĞIEVLER MAHALLESİNDEDİR. 25 LİK PAFTADAKİ YERİ: G36-D3
36°8'58" Doğu - 40°32'30" Kuzey
YAĞIŞ ALANI: 21.00 km2 YAKLAŞIK KOT: 815 m
GÖZLEM SÜRESİ: 01.09.1997 - 30.09.2006

			ÖLÇÜLEN AKIMLAR		
EŞEL SEVİYESİ (CM)	AKIM(M3/SN)	TARİH	EŞEL SEVİYESİ (CM)	AKIM(M3/SN)	TARİH
10	0,012	13.07.2006	8	0,007	07.02.2006
8	0,006	17.08.2006	9	0,008	08.03.2006
8	0,004	27.09.2006	11	0,017	05.04.2006
10	0,012	26.10.2005	12	0,036	03.05.2006
9	0,008	24.11.2005	12	0,026	24.05.2006
10	0,009	20.12.2005	12	0,031	15.06.2006

14. Yesilirmak Havzasi
D14A142 ÖZ D. ÇİME

YERİ: TOKAT-SULUSARAY İLÇE MERKEZİNDEN ÇİME KÖYÜNE AYRILAN YOLUN 4. KM ÇİME KÖYÜNDEDİR. 25 LİK PAFTADAKİ YERİ: İ36-A1
36°5'11" Doğu - 39°57'45" Kuzey
YAĞIŞ ALANI: 27.00 km2 YAKLAŞIK KOT: 1090 m
GÖZLEM SÜRESİ: 26.08.1997 - 30.09.2006

ÖLÇÜLEN AKIMLAR

EŞEL SEVİYESİ (CM)	AKIM(M3/SN)	TARİH	EŞEL SEVİYESİ (CM)	AKIM(M3/SN)	TARİH
3	0,000	17.07.2006	16	0,047	22.02.2006
2	0,000	14.08.2006	17	0,093	27.03.2006
0	0,000	12.09.2006	18	0,080	19.04.2006
15	0,028	27.10.2005	18	0,063	17.05.2006
16	0,051	21.02.2006	9	0,019	15.06.2006

14. Yesilirmak Havzasi

D14A143 ERİKLİ D. TÜRKDERBENDİ

YERİ: ZİLE-ÇEKEREK YOLUNUN 25. KM SAĞA AYRILAN YOLUN 10. KM TÜRKDERBENDİ KÖYÜNDEDİR. 25 LİK PAFTADAKİ YERİ: H35-A4
35°35'42" Doğu - 40°15'30" Kuzey
YAĞIŞ ALANI: 12.10 km2 YAKLAŞIK KOT: 885 m
GÖZLEM SÜRESİ: 13.08.1997 - 30.09.2006

14. Yesilirmak Havzasi

D14A144 BEĞERGEN D. AKARÇAY

YERİ: TOKAT-ALMUS BARAJI BATISINDAKİ AKARÇAY KASABASI MERKEZİNDEDİR. 25 LİK PAFTADAKİ YERİ: H38-A4
37°2'23" Doğu - 40°22'0" Kuzey
YAĞIŞ ALANI: 16.40 km2 YAKLAŞIK KOT: 928 m
GÖZLEM SÜRESİ: 12.08.1997 - 30.09.2006

ÖLÇÜLEN AKIMLAR

EŞEL SEVİYESİ (CM)	AKIM(M3/SN)	TARİH	EŞEL SEVİYESİ (CM)	AKIM(M3/SN)	TARİH
22	0,028	31.10.2005	27	0,125	29.11.2005
31	0,173	17.02.2006	36	0,173	17.02.2006
21	0,015	12.07.2006	30	0,139	24.03.2006
20	0,000	11.08.2006	38	0,517	06.04.2006
0	0,000	13.09.2006	33	0,386	10.05.2006
24	0,028	31.10.2005	26	0,093	12.06.2006

14. Yesilirmak Havzasi

D14A149 HULAR D. ÇAMAĞZI

YERİ: TOKAT-NİKSAR KARAYOLUNUN 16. KM ÇAMAĞIZI KÖYÜNÜN 2.5 KM KUZEYBATISINDADIR. 25 LİK PAFTADAKİ YERİ: H37-A2
36°39'42" Doğu - 40°26'16" Kuzey
YAĞIŞ ALANI: 44.20 km2 YAKLAŞIK KOT: 742 m
GÖZLEM SÜRESİ: 01.10.1997 - 30.09.2006

ÖLÇÜLEN AKIMLAR

EŞEL SEVİYESİ (CM)	AKIM(M3/SN)	TARİH	EŞEL SEVİYESİ (CM)	AKIM(M3/SN)	TARİH
5	0,093	29.11.2005	0	0,295	13.04.2006
0	0,329	22.03.2006	0	0,320	15.05.2006
0	0,000	13.04.2006	0	0,034	04.06.2006
0	0,000	15.05.2006	0	0,009	12.07.2006
0	0,000	04.06.2006	0	0,000	10.08.2006

14. Yesilirmak Havzasi

D14G152 YENİHAYAT BARAJI GÖL GÖZLEM

YERİ: ÇORUM-SUNGURLU YOLUNUN 20 KM. SİNDEKİ HAMDİKÖYDEN YAKLAŞIK 6 KM. SONRA YENİHAYAT BARAJINA VARILIR.İSTASYON KÖYE 500 M. MESAFEDEDİR.
34°40'3" Doğu-40°23'39" Kuzey
YAĞIŞ ALANI: 202.00 km2 YAKLAŞIK KOT: 908 m
GÖZLEM SÜRESİ: 01.07.1998 - 30.09.2006(5 Yıl)

14. Yesilirmak Havzasi

D14A154 BAHÇEBAŞI D. GÖÇENLİ

YERİ: YILDIZTEPE-ARTOVA KARAYOLUNUN 15 KM SOLA AYRILAN STABLİZE YOLUN 3 KM GÖÇENLİ KÖYÜNÜN KUZEY TARAFINDAKİ MAHALLENİN ALTINDADIR. 25 LİK PAFTADAKİ YERİ: H36-D1
36°4'12" Doğu - 40°10'49" Kuzey
YAĞIŞ ALANI: 160.30 km2 YAKLAŞIK KOT: 953 m
GÖZLEM SÜRESİ: 10.10.2001 - 30.09.2006

ÖLÇÜLEN AKIMLAR

EŞEL SEVİYESİ (CM)	AKIM(M3/SN)	TARİH	EŞEL SEVİYESİ (CM)	AKIM(M3/SN)	TARİH
22	0,161	19.09.2006	20	0,107	13.12.2005
23	0,087	19.07.2006	21	0,163	24.02.2006
20	0,040	15.08.2006	24	0,219	29.03.2006
16	0,020	19.09.2006	22	0,187	18.04.2006
22	0,145	06.10.2005	23	0,156	16.05.2006

14. Yesilirmak Havzasi

D14A158 DEĞİRMEN D. ZİYARET BARAJI

YERİ: AMASYA MERKEZİNİN 3 KM GÜNEYİNDEKİ ZİYARET KASABASINA 2.5 KM MESAFEDEKİ ZİYARET BARAJININ MEMBASINDADIR.
25 LİK PAFTADAKİ YERİ: G35-C1
35°51'4" Doğu - 40°42'23" Kuzey
YAĞIŞ ALANI: 20.30 km2 YAKLAŞIK KOT: 570 m
GÖZLEM SÜRESİ: 01.07.2003 - 30.09.2006

ÖLÇÜLEN AKIMLAR

EŞEL SEVİYESİ (CM)	AKIM(M3/SN)	TARİH	EŞEL SEVİYESİ (CM)	AKIM(M3/SN)	TARİH
0	0,000	12.07.2006	29	0,057	07.02.2006
0	0,000	17.08.2006	29	0,099	08.03.2006

0	0,000	28.09.2006	28	0,081	05.04.2006
28	0,050	26.10.2005	25	0,032	01.05.2006
28	0,050	24.11.2005	24	0,015	23.05.2006
28	0,063	20.12.2005	26	0,049	15.06.2006

14. Yesilirmak Havzasi
D14A160 SİLİSÖZÜ D. MERTEKLİ

YERİ: TOKAT-ARTOVA-BOZTEPE KARAYOLUNUN 22. KM SİNDEKİ MERTEKLİ KÖYÜ GİRİŞİNDEDİR. 25 LİK PAFTADAKİ YERİ: H36-D1
36°6'43" Doğu - 40°8'39" Kuzey
YAĞIŞ ALANI: 114.50 km2 YAKLAŞIK KOT: 1035 m
GÖZLEM SÜRESİ: 26.10.2004 - 30.09.2006

ÖLÇÜLEN AKIMLAR

EŞEL SEVİYESİ (CM)	AKIM(M3/SN)	TARİH	EŞEL SEVİYESİ (CM)	AKIM(M3/SN)	TARİH
0	0,000	19.07.2006	21	0,212	21.02.2006
0	0,000	15.08.2006	21	0,190	24.02.2006
0	0,000	19.09.2006	23	0,286	29.03.2006
16	0,145	21.10.2005	24	0,315	18.04.2006
16	0,124	13.12.2005	23	0,260	16.05.2006

15. Kizilirmak Havzasi
D15G020 BALIK GÖLÜ YÖRÜKLER

YERİ: SAMSUN-BAFRA YOLUNUN 42. KM SİNDE ENGİZ KÖYÜNÜN 4. KM SİNDEKİ YÖRÜKLER KÖYÜ YAKININDAKİ GÖLDEDİR. 25 LİK PAFTADA YERİ: E36-D4 34°4'49"
Doğu-41°31'46" Kuzey
YAĞIŞ ALANI: 320.00 km2 YAKLAŞIK KOT: 1 m
GÖZLEM SÜRESİ: 01.10.1959 - 30.09.2006

15. Kizilirmak Havzasi
D15A108 KALEYCİK DERESI DOYDUK

YERİ: 1979KOZAKLI İLÇESİNE 9KM MESAFEDEKİ DOYDUK KÖYÜNDEDİR.
34°45'2" Doğu - 39°11'28" Kuzey
YAĞIŞ ALANI: 427.50 km2 YAKLAŞIK KOT: 1028 m
GÖZLEM SÜRESİ: 01.06.1966 - 30.09.2005

ÖLÇÜLEN AKIMLAR

EŞEL SEVİYESİ (CM)	**AKIM(M3/SN)**	**TARİH**	**EŞEL SEVİYESİ (CM)**	**AKIM(M3/SN)**	**TARİH**
12	**0,019**	**11.10.2005**	**17**	**0,086**	**03.04.2006**
29	**0,008**	**24.11.2005**	**18**	**0,057**	**16.05.2006**
15	**0,009**	**16.12.2005**	**0**	**0,000**	**09.06.2006**
16	**0,083**	**06.01.2006**	**0**	**0,000**	**13.07.2006**
17	**0,087**	**24.02.2006**	**0**	**0,000**	**25.08.2006**
19	**0,102**	**21.03.2006**	**0**	**0,000**	**21.09.2006**

15. Kizilirmak Havzasi
D15A190 Cenderözü S. Sahinoglu

YERİ: ÇİÇEKDAĞINDAN ŞAHİNOĞLU KÖYÜNE GİDİLİR.İSTASYON REGÜLATÖRÜNALTINDAKİ KÖPRÜDEDİR.
34°29'36" Doğu - 39°33'59" Kuzey
YAĞIŞ ALANI: 350.30 km2 YAKLAŞIK KOT: 855 m
GÖZLEM SÜRESİ: 01.11.1979 - 30.09.2006

ÖLÇÜLEN AKIMLAR

EŞEL SEVİYESİ (CM)	AKIM(M3/SN)	TARİH	EŞEL SEVİYESİ (CM)	AKIM(M3/SN)	TARİH
33	0,079	10.10.2005	31	0,088	13.04.2006
26	0,168	08.11.2005	41	0,217	02.05.2006
34	0,114	21.12.2005	29	0,010	08.06.2006
34	0,119	17.01.2006	36	0,053	04.07.2006
36	0,190	27.02.2006	28	0,003	07.08.2006
36	0,191	23.03.2006	28	0,004	07.09.2006

15. Kizilirmak Havzasi
D15A208 DEGİRMENÖZÜ SUYU DEGİRMENÖZÜ

YERİ: KIRŞEHİRİN KAMAN İLÇESİNDEN SAĞA DÖNÜLÜRİSTASYON 5 KM SONRA İNZİLOĞLU ÇİTLİĞİNE VARMADAN SOLDADIR.
33°43'58" Doğu - 39°25'37" Kuzey
YAĞIŞ ALANI: 37.20 km2 YAKLAŞIK KOT: 960 m
GÖZLEM SÜRESİ: 01.04.1984 - 30.09.2006

ÖLÇÜLEN AKIMLAR

EŞEL SEVİYESİ (CM)	AKIM(M3/SN)	TARİH	EŞEL SEVİYESİ(CM)	AKIM(M3/SN)	TARİH
0	0,000	12.10.2005	22	0,076	12.04.2006
17	0,048	08.11.2005	40	0,211	03.05.2006
19	0,114	14.12.2005	18	0,040	07.06.2006
18	0,062	18.01.2006	18	0,036	12.07.2006
34	0,194	22.02.2006	3	0,057	15.08.2006

15. Kizilirmak Havzasi
D15A217 Korudere Fehimli Göleti

YERİ: KAYSERİ-BOĞAZLIYAN YOLUNUN 60.KM SİNDEKİ KORU DERESİ ÜZERİNDEDİR.

35°7'6" Doğu - 39°5'8" Kuzey
YAĞIŞ ALANI: 223.80 km2 YAKLAŞIK KOT: 1074 m
GÖZLEM SÜRESİ: 01.10.1986 - 30.09.2006

ÖLÇÜLEN AKIMLAR					
EŞEL SEVİYESİ (CM)	AKIM(M3/SN)	TARİH	EŞEL SEVİYESİ (CM)	AKIM(M3/SN)	TARİH
0	0,000	21.06.2006	0	0,000	20.12.2005
0	0,000	06.07.2006	0	0,000	05.01.2006
0	0,000	09.08.2006	0	0,000	06.02.2006
0	0,000	12.09.2006	0	0,000	10.03.2006
0	0,000	19.10.2005	1	0,005	11.04.2006
0	0,000	24.11.2005	2	0,010	18.05.2006

15. Kizilirmak Havzasi
D15G230 GÜLDÜRCEK BARAJI GÖL GÖZLEM

YERİ: ÇANKIRI İLİ ORTA İLÇESİ KARGA KÖYÜ MEVKİNDEDİR.
32°57'30" Doğu-40°34'0" Kuzey
YAĞIŞ ALANI: 140.70 km2 YAKLAŞIK KOT: 1471 m
GÖZLEM SÜRESİ: 01.12.1989 - 30.09.2006(10 Yıl)

15. Kizilirmak Havzasi
D15A287 EĞİNOĞLU DERESİ İNCESU

YERİ: ÇORUM OSMANCIK YOLUNUN 45.KM SİNDE İNCESU KÖYÜNÜN 3 KM DOĞUSUNDA EĞİNOĞLU DERESİ ÜZERİNDEDİR.
34°58'3" Doğu - 40°53'24" Kuzey
YAĞIŞ ALANI: 30.25 km2 YAKLAŞIK KOT: 720 m
GÖZLEM SÜRESİ: 15.12.1998 - 30.09.2006

15. Kizilirmak Havzasi
D15A293 Çorak D. Y.Sarikaya Göl.Giris

YERİ: KAYSERİ BOGAZLIYAN YOZGAT YOLUNUN 110 KM DE YUKARI SARIKAYAKASABASININ YAKININDADIR.
35°9'41" Doğu - 39°24'6" Kuzey
YAĞIŞ ALANI: 22.60 km2 YAKLAŞIK KOT: 1176 m
GÖZLEM SÜRESİ: 01.10.2000 - 30.09.2006

15. Kizilirmak Havzasi
D15A297 KARASU ILETİM KANALI MOLU HES

YERİ: KAYSERİ-ANKARA KARAYOLUNUN 22 KM.REGÜLATÖRÜN 0.5 KM.MANSABINDAKİ BETON KÖPRÜNÜN ALTINDADIR.HER MEVSİMDE GİDİLİR.
35°17'36" Doğu - 38°46'20" Kuzey
YAĞIŞ ALANI: 0.00 km2 YAKLAŞIK KOT: 1022 m
GÖZLEM SÜRESİ: 25.01.2002 - 30.09.2006

ÖLÇÜLEN AKIMLAR					
EŞEL SEVİYESİ (CM)	AKIM(M3/SN)	TARİH	EŞEL SEVİYESİ (CM)	AKIM(M3/SN)	TARİH
10.70	3.414	11.10.2005	11.50	3.973	16.03.2006
13.30	4.891	19.10.2005	12.50	4.334	28.03.2006
11.90	3.454	01.11.2005	11.10	3.735	14.04.2006
12.30	3.796	30.12.2005	10.90	3.614	28.04.2006
10.40	3.466	30.01.2006	10.20	3.287	26.05.2006
12	4.192	07.02.2006	89	2.554	14.06.2006

15. Kizilirmak Havzasi
D15A307 YILDIZ IRMAĞI YUKARI YILDIZLI

YERİ: SİVAS MERKEZ Y.YILDZLI KÖYÜNÜN YAKININDADIR
36°46'14" Doğu - 39°45'56" Kuzey
YAĞIŞ ALANI: 1408.00 km2 YAKLAŞIK KOT: 1252 m
GÖZLEM SÜRESİ: 01.10.2005 - 30.09.2006

15. Kizilirmak Havzasi
D15G309 SEYFE KAYNAĞI VE HORLA KAYNAĞI SEYFE GÖLÜ

YERİ: KIRSEHIR-MUCUR ILCESINDEN SAGA AYRILAN MALYA DUÇ YOLUNUN17 KM.SINDEKI HORLA KOYUNUN KUZEYDOGUSUNDADIR.
34°22'14" Doğu-39°11'42" Kuzey
YAĞIŞ ALANI: 1430.00 km2 YAKLAŞIK KOT: 1115 m

16. Konya Kapali Havzasi
D16A001 Beysehir Kanali Incesu

YERİ: SEYDİŞEHİR-BOZKIR-KESECİK KOYÜNE 2 KM MESAFEDEDİR. (LİM)
31°35'0" Doğu - 37°26'0" Kuzey
YAĞIŞ ALANI: 1000.00 km2 YAKLAŞIK KOT: 1101 m
GÖZLEM SÜRESİ: 01.01.1959 - 30.09.2006

16. Konya Kapali Havzasi
D16G016 Çavusçu G. Göl Gözlem

YERİ: ILGIN İLÇESİNİN 3.KM.DEKİ BELEDİYE SÖĞÜTLÜĞÜNDEDİR.
31°53'0" Doğu-38°19'0" Kuzey
YAĞIŞ ALANI: 603.00 km2 YAKLAŞIK KOT: 1019 m
GÖZLEM SÜRESİ: 01.04.1959 - 30.09.2006(44 Yıl)

16. Konya Kapali Havzasi
D16G042 Sille Brj. Göl Gözlem

YERİ: KONYA MERKEZ. 32°24'1" Doğu-37°55'43" Kuzey

YAĞIŞ ALANI: 26.00 km2 YAKLAŞIK KOT: 1342 m
GÖZLEM SÜRESİ: 05.11.1961 - 30.09.2006(34 Yıl)

16. Konya Kapali Havzasi
D16G043 Ayranci Brj. Göl Gözlem

YERİ: 33°43'46" Doğu-37°20'18" Kuzey
YAĞIŞ ALANI: ---- km2 YAKLAŞIK KOT: 1270 m
GÖZLEM SÜRESİ: 01.08.1962 - 30.09.2006(31 Yıl)

16. Konya Kapali Havzasi
D16G045 Apa Brj. Göl Gözlem

YERİ: KONYA HADIM YOLUNUN 53KM SINDEN SAGA AYRILAN YOLUNUN 10 KMSINDEKI APA BR GOLUNDEDIR
3°96'0" Doğu-41°5'1" Kuzey
YAĞIŞ ALANI: 6780.00 km2 YAKLAŞIK KOT: 0 m
GÖZLEM SÜRESİ: 11.12.1962 - 30.09.2005(37 Yıl)

16. Konya Kapali Havzasi
D16G047 Mamasin Brj. Göl Gözlem

YERİ: AKSARAY NEVŞEHİR YOLUNUN 10.KM.DEN SAĞA DÖNÜLÜR 5.KM SONRA BARAJA VARILIR.
34°8'0" Doğu-38°24'0" Kuzey
YAĞIŞ ALANI: 1383.00 km2 YAKLAŞIK KOT: 1085 m
GÖZLEM SÜRESİ: 22.02.1963 - 30.09.2006(39 Yıl)

16. Konya Kapali Havzasi
D16G050 Obruk G. Göl Gözlem

YERİ: KONYA AKSARAY YOLUNUN 70.KM.DEKİ KIZÖRENE VARILIR. SOLA OBRUK HANA DÖNÜLÜR.4.KM SONRA GÖLE VARILIR.
33°11'0" Doğu-38°10'0" Kuzey
YAĞIŞ ALANI: 0.03 km2 YAKLAŞIK KOT: 976 m
GÖZLEM SÜRESİ: 16.05.1963 - 30.09.2006(40 Yıl)

16. Konya Kapali Havzasi
D16G052 Timras Obrugu Göl G.(Gökhüyük)

YERİ: ÇUMRA GÖKHÜYÜK. 32°43'21" Doğu-37°28'53" Kuzey
YAĞIŞ ALANI: ---- km2 YAKLAŞIK KOT: 1007 m
GÖZLEM SÜRESİ: 01.10.1965 - 30.09.2006 (38 Yıl)

16. Konya Kapali Havzasi
D16G062 Hotamis G. Göl Gözlem

YERİ: 33°1'0" Doğu-37°30'0" Kuzey
YAĞIŞ ALANI: ---- km2 YAKLAŞIK KOT: 999 m
GÖZLEM SÜRESİ: 01.02.1965 - 30.09.2005(31 Yıl)

16. Konya Kapali Havzasi
D16G067 Gebere Brj. Göl Gözlem

YERİ: NİĞDE YEŞİLBURÇ-TEPEKÖY YOLUNA GİRİLİR YEŞİLBURÇ KÖYÜ GEÇİLDİKTEN SONRA SOLA DÖNÜLÜR. 2 KM SONRA GEBERE BARAJINA VARILIR
6°28'0" Doğu-42°27'0" Kuzey
YAĞIŞ ALANI: 17.40 km2 YAKLAŞIK KOT: 1698 m
GÖZLEM SÜRESİ: 01.12.1965 - 30.09.2006(33 Yıl)

16. Konya Kapali Havzasi
D16G073 Altinapa Brj. Göl Gözlem

YERİ: KONYA BEYŞEHİR YOLUNUN 20.KM SİNDEKİ ALTINAPA BARAJINDADIR.
32°19'0" Doğu-37°53'0" Kuzey
YAĞIŞ ALANI: 589.00 km2 YAKLAŞIK KOT: 1239.50 m
GÖZLEM SÜRESİ: 29.12.1966 - 30.09.2006(35 Yıl)

16. Konya Kapali Havzasi
D16G076 Gümüsler Brj. Göl Gözlem

YERİ: NİĞDE KAYSERİ YOLUNUN 10.KM.DE SAĞA GÜMÜŞLER KÖYÜ YOLUNAGİRİLİR SOLA DÖNEN YOL BARAJA ULAŞIR.
34°45'0" Doğu-38°0'0" Kuzey
YAĞIŞ ALANI: 69.20 km2 YAKLAŞIK KOT: 1350 m
GÖZLEM SÜRESİ: 01.05.1967 - 30.09.2006(35 Yıl)

16. Konya Kapali Havzasi
D16A088 Gödet Ç. Fisandun

YERİ: KARAMAN DEREKÖY MEVKİİ.
33°15'52" Doğu - 37°7'43" Kuzey
YAĞIŞ ALANI: 476.30 km2 YAKLAŞIK KOT: 1096 m
GÖZLEM SÜRESİ: 30.09.1995 - 30.09.2006

16. Konya Kapali Havzasi
D16A102 Ayranci Brj. Çikis

YERİ: KARAMAN AYRANCI.
33°43'21" Doğu - 37°20'29" Kuzey
YAĞIŞ ALANI: 1158.20 km2 YAKLAŞIK KOT: 1151 m
GÖZLEM SÜRESİ: - 30.09.1984-30.09.2006

16. Konya Kapali Havzasi
D16G112 Akgöl Göl Gözlem (Eregli)

YERİ: İstasyona Ait Adres Bilgisi Girilmemiştir.
33°45'11" Doğu-37°29'17" Kuzey
YAĞIŞ ALANI: 19.10 km2 YAKLAŞIK KOT: 1000 m
GÖZLEM SÜRESİ: 18.11.1976 - 30.09.2006

16. Konya Kapali Havzasi
D16A114 Topkaya Göleti Giris (Saçikara)

YERİ: KADINHANI SAÇIKARA KÖYÜ.
32°8'23" Doğu - 38°35'23" Kuzey
YAĞIŞ ALANI: 1400.70 km2 YAKLAŞIK KOT: 950 m
GÖZLEM SÜRESİ: 16.11.1976 - 30.09.2006

16. Konya Kapali Havzasi
D16G120 Sugla G. Göl Gözlem

YERİ: KONYA SEYDİŞEHİR ÇATMAKAYA KÖYÜNE VARILIR. KÖYÜN 2 KM YANIN-DAKİ ARVANA DÜDENİNDEDİR.
32°0'0" Doğu-37°16'0" Kuzey
YAĞIŞ ALANI: 5870.00 km2 YAKLAŞIK KOT: 1087.7710 m
GÖZLEM SÜRESİ: 01.08.1978 - 30.09.2006(20 Yıl)

16. Konya Kapali Havzasi
D16A123 Çigil D. Nafia Kan.

YERİ: KONYA ILGIN MERKEZ.
31°53'53" Doğu - 38°16'46" Kuzey
YAĞIŞ ALANI: ---- km2 YAKLAŞIK KOT: 1040 m
GÖZLEM SÜRESİ: 01.10.1978 - 30.09.2006

16. Konya Kapali Havzasi
D16G142 Ivriz Brj. Göl Gözlem

YERİ:EREĞLİ İVRİZ YOLUNDAN İVRİZ BARAJINA VARILIR.İVRİZ BARAJINDAN BÜTÜN İSTASYONLARA ULAŞIM VARDIR.
34°10'0" Doğu-37°27'0" Kuzey
YAĞIŞ ALANI: 325.00 km2 YAKLAŞIK KOT: 1129.30 m
GÖZLEM SÜRESİ: 01.10.1984 - 30.09.2006(18 Yıl)

16. Konya Kapali Havzasi
D16A143 Ivriz Brj. Çikis (Anayatak)

YERİ: İstasyona Ait Adres Bilgisi Girilmemiştir.
34°8'57" Doğu - 37°27'14" Kuzey
YAĞIŞ ALANI: 325.00 km2 YAKLAŞIK KOT: 1115 m
GÖZLEM SÜRESİ: 12.12.1984 - 30.09.2006

16. Konya Kapali Havzasi
D16A144 Ivriz Brj.Çikis Sol Ana Kanal

YERİ: EREĞLİ IVRIZ YOLU ÜZERI.
34°9'7" Doğu - 37°26'43" Kuzey
YAĞIŞ ALANI: 1000.00 km2 YAKLAŞIK KOT: 1127 m
GÖZLEM SÜRESİ: 16.04.1986 - 30.09.2006

16. Konya Kapali Havzasi
D16A145 Ivriz Brj.Çikis Sag Ana Kanal

YERİ: EREĞLİ ZANAPA YOLU ÜZERI.
34°9'31" Doğu - 37°27'15" Kuzey
YAĞIŞ ALANI: 1000.00 km2 YAKLAŞIK KOT: 1127 m
GÖZLEM SÜRESİ: 01.10.1984 - 30.09.2006

16. Konya Kapali Havzasi
D16G153 Gödet Brj. Göl Gözlem

YERİ: KARAMANDAN DEREKÖYE GİDİLİR. DEREKÖYDEN 1 KM SONRA BARAJGÖVDESİNDEDİR.
33°16'23" Doğu-37°7'7" Kuzey
YAĞIŞ ALANI: --- km2 YAKLAŞIK KOT: 1120.60 m
GÖZLEM SÜRESİ: 01.10.1991 - 30.09.2006(7 Yıl)

16. Konya Kapali Havzasi
D16G157 Tuz G. Göl Gözl.(Yavsan Tuzlasi)

YERİ: CİHANBEYLI TUZ GÖLÜ IŞLETMESI. 33°11'54" Doğu-38°47'0" Kuzey
YAĞIŞ ALANI: ---- km2 YAKLAŞIK KOT: 903 m
GÖZLEM SÜRESİ: ------ - (0 Yıl)

16. Konya Kapali Havzasi
D16A162 Zanapa Ç. Dedeli

YERİ:
34°17'51" Doğu - 37°25'8" Kuzey
YAĞIŞ ALANI: ---- km2 YAKLAŞIK KOT: 1310 m
GÖZLEM SÜRESİ: 01.10.2005 - 30.09.2006

16. Konya Kapali Havzasi
D16A164 T3 Tahliye Kan. Adabag

YERİ: EREĞLİ ADABAĞ
33°51'37" Doğu - 37°30'31" Kuzey
YAĞIŞ ALANI: ---- km2 YAKLAŞIK KOT: 1000 m
GÖZLEM SÜRESİ: 01.10.1997 - 30.09.2006

16. Konya Kapali Havzasi
D16G169 Beysehir G. Göl Gözlem (Akburun)

YERİ: BEYŞEHİR AKBURUN POMPASINDA BULUNMAKTADIR.
31°35'35" Doğu-37°46'53" Kuzey
YAĞIŞ ALANI: ---- km2 YAKLAŞIK KOT: 1126 m

GÖZLEM SÜRESİ: 01.10.2003 - 30.09.2006 (3 Yıl)

17. Dogu Akdeniz Havzasi
D17A043 GÜLEK D. ÇAMALAN

YERİ: ADANA-ANKARA KARAYOLU ÇAMLIYAYLA AYRIMI 1 KM.SİNDEKİ GÜLEK DERESİ ÜZERINDE KÖPRÜNÜN 250 M MEMBASINDADIR.
34°48'39" Doğu - 37°9'38" Kuzey
YAĞIŞ ALANI: 195.00 km2 YAKLAŞIK KOT: 560 m
GÖZLEM SÜRESİ: 01.10.1994 - 30.09.2006

17. Dogu Akdeniz Havzasi
D17A044 SOĞUKSU AYDINCIK

YERİ: MERSİN İLİ AYDINCIK İLÇESİ SOĞUKSU MEVKİİNDEDİR.
33°17'43" Doğu - 36°8'18" Kuzey
YAĞIŞ ALANI: 31.80 km2 YAKLAŞIK KOT: 15 m
GÖZLEM SÜRESİ: 01.11.1994 - 30.09.2006

ÖLÇÜLEN AKIMLAR

EŞEL SEVİYESİ (CM)	AKIM(M3/SN)	TARİH	EŞEL SEVİYESİ (CM)	AKIM(M3/SN)	TARİH
42	0,279	17.10.2005	75	3,317	07.04.2006
59	0,717	14.11.2005	61	1,324	12.05.2006
62	0,932	14.12.2005	65	1,691	09.06.2006
61	1,031	06.01.2006	61	0,896	17.07.2006
104	7,676	17.02.2006	63	1,114	09.08.2006
92	5,321	10.03.2006	58	0,556	06.09.2006

17. Dogu Akdeniz Havzasi
D17A052 PAMUKLUK Ç. ÇAMLIYAYLA

YERİ: MERSİN İLİ ÇAMLIYAYLA İLÇESİ CEHENNEM DERE DEĞİRMENİ MEVKİİNDE BULUNAN PAMUK HES REGÜLATÖRÜNÜN 30 M. MANSABINDADIR.
34°36'30" Doğu - 37°7'0" Kuzey
YAĞIŞ ALANI: 395.00 km2 YAKLAŞIK KOT: 480 m
GÖZLEM SÜRESİ: 01.10.2002 - 30.09.2006

18. Seyhan Havzasi
D18A030 Zamanti Ir. Mustafa Oruç

YERİ: YAHYALI BÜYÜKÇAYIR KÖYLERİ YOLUNUN 68.KM SİNDE DEĞİRMENOCAĞINDADIR.
35°26'0" Doğu - 37°47'0" Kuzey
YAĞIŞ ALANI: 7754.50 km2 YAKLAŞIK KOT: 626 m
GÖZLEM SÜRESİ: 13.01.1989 - 30.09.2006

18. Seyhan Havzasi
D18A031 ZAMANTI N. GÖKTAŞ

YERİ: ALADAĞ İLÇESİNİN 35 KM KUZEYİNDEKİ KÖYKENARI KÖYÜ YAKINILARINDADIR.
35°28'5" Doğu - 37°43'51" Kuzey
YAĞIŞ ALANI: 8921.50 km2 YAKLAŞIK KOT: 500 m
GÖZLEM SÜRESİ: 01.06.1988 - 30.09.2006

18. Seyhan Havzasi
D18A045 SEYHAN N. SANTRAL REG.

YERİ: TUZLA-TARSUS YOLUNUN SALGEÇİDİ MEVKİİNDE YENİ YAPILAN SEYHAN NEHRİ KÖPRÜSÜNDEDİR.
35°3'50" Doğu - 36°47'8" Kuzey
YAĞIŞ ALANI: 19352.00 km2 YAKLAŞIK KOT: 20 m
GÖZLEM SÜRESİ: 01.03.1996 - 30.09.2006

18. Seyhan Havzasi
D18A046 Dogan Ç. Aladag

YERİ: Aladağ - Darıçukuru köyü yolunun 10 km' sindeki köprünün 100 m mansabındadır.
35°59'18" Doğu - 38°47'36" Kuzey
YAĞIŞ ALANI: 463.00 km2 YAKLAŞIK KOT: 570 m
GÖZLEM SÜRESİ: 01.10.1998 - 30.09.2006

ÖLÇÜLEN AKIMLAR

EŞEL SEVİYESİ (CM)	AKIM(M3/SN)	TARİH	EŞEL SEVİYESİ (CM)	AKIM(M3/SN)	TARİH
82	0,272	06.10.2005	124	10,032	04.04.2006
89	1,321	09.11.2005	97	3,278	02.05.2006
92	1,308	06.12.2005	81	0,736	15.06.2006
91	2,015	03.01.2006	77	0,593	18.07.2006
108	8,417	21.02.2006	74	0,548	09.08.2006

18. Seyhan Havzasi
D18G052 ZAMANTI IRMAĞI BAHÇELİK BARAJI

YERİ: KAYSERİ PINARBAŞI KARAYOLU İLE BAHÇECİK KÖYÜ MEMBAINDA BAHÇELİK BARAJINDADIR.
36°17'39" Doğu-38°40'21" Kuzey
YAĞIŞ ALANI: 2778.00 km2 YAKLAŞIK KOT: 1505 m

20. Ceyhan Havzasi
D20A007 Hurman S. Kuskayasi

YERİ: 1982K.Maraş Afşin ilçesine 20 km mesafedeki Kuşkayası Köyü civarındadır.

37°2'0" Doğu - 38°17'0" Kuzey
YAĞIŞ ALANI: 2084.00 km2 YAKLAŞIK KOT: 1150 m
GÖZLEM SÜRESİ: 08.08.1961 - 30.09.2006

20. Ceyhan Havzasi
D20A013 Andirin S. Tokmakli

YERİ: KADİRLİ-ANDIRIN YOLUNUN 21.KM.SİNDEKİ SAGA AYRILAN ABAZALI KÖYÜ YOLUNUN 9.KM.SİNDEKİ TOKMAKLI KÖYÜNDEDİR.
36°19'37" Doğu - 37°26'53" Kuzey
YAĞIŞ ALANI: 205.00 km2 YAKLAŞIK KOT: 205 m
GÖZLEM SÜRESİ: 11.08.1961 - 30.09.2006

20. Ceyhan Havzasi
D20A016 Kömürsuyu Alislibucak

YERİ: GÖKSÜN İLCESİNE 8.5 KM MESAFEDE ALIÇLIBUCAK KÖYÜNDEDIR.
36°31'0" Doğu - 38°5'0" Kuzey
YAĞIŞ ALANI: 291.00 km2 YAKLAŞIK KOT: 1386 m
GÖZLEM SÜRESİ: 15.08.1961 - 30.09.2006

20. Ceyhan Havzasi
D20A017 Aksu Çayi Köprüagzi

YERİ: K.MARAŞ-G.ANTEP YOLUNUN KAPIÇAM MEVKİSİNDEN SAĞA AYRILAN YO-LUN 15. KM SINDE DEMIRCILER KÖYÜNDEDIR.
37°1'0" Doğu - 37°21'0" Kuzey
YAĞIŞ ALANI: 1740.00 km2 YAKLAŞIK KOT: 560 m
GÖZLEM SÜRESİ: 12.12.1970 - 30.09.2006

20. Ceyhan Havzasi
D20G028 Inekli G. Göl Gözlem

YERİ: GÖLBAŞI PAZARCIK YOLUNUN 10. KM.SİNDEN SAĞA AYRILAN YOLUN 3. KM.SİNDEKİ DDY ÇELİK İSTASYONU CİVARINDADIR.
37°32'35" Doğu-37°45'27" Kuzey
YAĞIŞ ALANI: 196.60 km2 YAKLAŞIK KOT: 872 m

20. Ceyhan Havzasi
D20G029 AZAPLI G. Göl Gözlem

YERİ: GÖLBAŞI İLÇESI AZAPLI KÖYÜNDEDIR.
37°33'0" Doğu-37°45'0" Kuzey
YAĞIŞ ALANI: 112.00 km2 YAKLAŞIK KOT: 874 m

20. Ceyhan Havzasi
D20G030 Gölbasi G. Göl Gözlem

YERİ: GÖLBAŞI MESLEK YÜKSEK OKULU İÇERISINDEDIR. 37°39'0" Doğu-37°47'40" Kuzey
YAĞIŞ ALANI: 60.20 km2 YAKLAŞIK KOT: 881 m

20. Ceyhan Havzasi
D20A031 Gölbasi Gölü Çikis

YERİ: GÖLBAŞI İLÇESİNE 1 KM MESAFEDEKI GÖLBAŞI GÖLÜ ÇIKIŞININ 500M. MANSABINDADIR.
37°38'0" Doğu - 37°47'0" Kuzey
YAĞIŞ ALANI: 62.00 km2 YAKLAŞIK KOT: 882 m
GÖZLEM SÜRESİ: 15.08.1968 - 30.09.2006

20. Ceyhan Havzasi
D20A036 Körsulu D. Sisne

YERİ: ANDIRINA 28 KM MESAFEDEKİ SISNE KÖYÜNDEDIR.
36°29'0" Doğu - 37°43'0" Kuzey
YAĞIŞ ALANI: 150.80 km2 YAKLAŞIK KOT: 1250 m
GÖZLEM SÜRESİ: 15.05.1971 - 30.09.2006

20. Ceyhan Havzasi
D20A045 KIRK S. ESKİMANTAŞ KÖP.

YERİ: KOZAN - ESKİMANTAŞ KÖYÜ YOLUNUN 18 KM SİNDEKİ KÖPRÜNÜN 100 M MANSABINDADIR.
35°53'32" Doğu - 37°32'7" Kuzey
YAĞIŞ ALANI: 170.00 km2 YAKLAŞIK KOT: 276 m
GÖZLEM SÜRESİ: 01.10.1975 - 30.09.2006

20. Ceyhan Havzasi
D20A047 Aksu Ç. Haci Musatafa Çiftl.

YERİ: K.Maraş Türkoğlu karayolunun 9.km sinde eski karayolununköprü ayağındadır.
36°54'22" Doğu - 37°1'5" Kuzey
YAĞIŞ ALANI: 2787.30 km2 YAKLAŞIK KOT: 455 m
GÖZLEM SÜRESİ: 14.08.1979 - 30.09.2006

ÖLÇÜLEN AKIMLAR

EŞEL SEVİYESİ (CM)	AKIM(M3/SN)	TARİH	EŞEL SEVİYESİ (CM)	AKIM(M3/SN)	TARİH
53	8.553	04.10.2005	54	7.425	09.12.2005
57	8.262	11.11.2005	72	8.756	06.01.2006

20. Ceyhan Havzasi
D20A049 Erkenez Ç. Bulanik

YERİ: K.Maraş Bulanık Köyünün 2 km güney batısındadır.

37°7'0" Doğu - 37°34'0" Kuzey
YAĞIŞ ALANI: 119.00 km2 YAKLAŞIK KOT: 725 m
GÖZLEM SÜRESİ: 21.12.1982 - 30.09.2006

20. Ceyhan Havzasi
D20A052 Findik D. Findik
YERİ: K.MARAŞ-ELBSTAN KARAYOLUNUN 117. KM.SİNDE FINDIK KÖYÜ YOLAYRIMINA 50 M. MESAFEDEKI ESKI KÖPRÜ AYAĞINDADIR.
36°43'0" Doğu - 38°4'0" Kuzey
YAĞIŞ ALANI: 23.00 km2 YAKLAŞIK KOT: 1284 m
GÖZLEM SÜRESİ: 01.10.1983 - 30.09.2006

20. Ceyhan Havzasi
D20A055 Zeytin D. Süleymanli
YERİ: K.MARAŞ-KAYSERİ YOLUNUN 34.KM SINDEN SAĞA AYRILAN SÜLEYMANLIYOLUNDA KANLI KÖPRÜSÜNÜN 100 M. MANSABINDADIR
36°50'0" Doğu - 37°52'0" Kuzey
YAĞIŞ ALANI: 111.60 km2 YAKLAŞIK KOT: 850 m
GÖZLEM SÜRESİ: 16.08.1984 - 30.09.2006

20. Ceyhan Havzasi
D20A060 Kisik D. Kisik
YERİ: K.MARAŞ-MALATYA YOLUNUN 70. KMSİNDEN SOLA AYRILAN KISIK KÖ-YÜ YOLUNUN 12.KM SINDEDIR.
37°23'0" Doğu - 37°37'0" Kuzey
YAĞIŞ ALANI: 131.50 km2 YAKLAŞIK KOT: 950 m
GÖZLEM SÜRESİ: 01.12.1984 - 30.09.2006

20. Ceyhan Havzasi
D20A061 Imali D. Türkoglu
YERİ: K.MARAŞ-ADANA KARAYOLU ÜZERİNDEKI TÜRKOĞLU İILÇESININ IÇINDEKI KÖPRÜDEN SAĞA AYRILDIKTAN SONRA 300 M. ILERIDEDIR.
36°28'32" Doğu - 37°28'32" Kuzey
YAĞIŞ ALANI: 64.40 km2 YAKLAŞIK KOT: 500 m
GÖZLEM SÜRESİ: 01.01.1987 - 30.09.2006

20. Ceyhan Havzasi
D20A064 Mizmilli Ç. Bertizler Obasi
YERİ: K.Maraş-G.Antep karayolunun Kapıçam Mevkinden sağa ayrıldık-tan sonra 20.km ileride Bertizler Obasındadır.
37°3'0" Doğu - 37°5'26" Kuzey
YAĞIŞ ALANI: 307.00 km2 YAKLAŞIK KOT: 535 m
GÖZLEM SÜRESİ: 01.10.1987 - 30.09.2006

20. Ceyhan Havzasi
D20A066 Sögütlü Ç. Karahasanus.
YERİ: Elbistan-Malatya karayolunun 30.km den sağa ayrılan stabilize yolun 17.km sindeki Karahasanuşağı Köyündedir.
37°37'12" Doğu - 38°9'35" Kuzey
YAĞIŞ ALANI: 150.00 km2 YAKLAŞIK KOT: 1455 m
GÖZLEM SÜRESİ: 15.10.1987 - 30.09.2006

20. Ceyhan Havzasi
D20A067 Hasan Ali D. Hasan Ali K.
YERİ: Elbistan-Malatya karayolunun 30. km sinden sağa ayrılan sta-bilize yolun 17.km sindeki Karahasanuşağı Köyündedir.
37°36'57" Doğu - 38°10'23" Kuzey
YAĞIŞ ALANI: 63.86 km2 YAKLAŞIK KOT: 1435 m
GÖZLEM SÜRESİ: 03.05.1990 - 30.09.2006

20. Ceyhan Havzasi
D20A070 Baglama D. Bertizler Oba.
YERİ: Türkoğlu-Narlı yolu üzerinde Bertizler obasındadır
37°7'30" Doğu - 37°16'53" Kuzey
YAĞIŞ ALANI: 1.00 km2 YAKLAŞIK KOT: 538 m
GÖZLEM SÜRESİ: 10.05.1991 - 30.09.2006

20. Ceyhan Havzasi
D20A074 TEKİR DERESI ALİŞAR (KISIK HES)
YERİ: TEKİR KASABASI ILE KISIK MAHALLESI ARASINDAKI YOLUN 1,5. KM'SINDEDIR.
36°37'59" Doğu - 37°52'30" Kuzey
YAĞIŞ ALANI: 89.60 km2 YAKLAŞIK KOT: 992 m
GÖZLEM SÜRESİ: 01.10.1995 - 30.09.2006

21. Firat Havzasi
D21A004 MURAT NEHRİ DİYADİN
YERİ: AĞRI İLİ DİYADİN İLÇESİNİN 500 M AŞAĞISINDADIR.
43°40'5" Doğu - 39°32'9" Kuzey
YAĞIŞ ALANI: 713.00 km2 YAKLAŞIK KOT: 1857 m
GÖZLEM SÜRESİ: 01.10.1986 - 30.09.2006

21. Firat Havzasi
D21A026 Keysun Ç. Körpinar

YERİ: Besni ilçesine 36 km mesafedeki Keysun Bucagındadır.
37°51'0" Doğu - 37°34'0" Kuzey
YAĞIŞ ALANI: 128.00 km2 YAKLAŞIK KOT: 585 m
GÖZLEM SÜRESİ: 28.06.1959 - 30.09.2006

21. Firat Havzasi
D21A041 PERİ S. SELENK KÖPRÜSÜ

YERİ: KIGI BINGOL YOLUNUN 11.KM.SİNDEDIR(J44-B4)
40°22'13" Doğu - 39°17'9" Kuzey
YAĞIŞ ALANI: 2062.00 km2 YAKLAŞIK KOT: 1154 m
GÖZLEM SÜRESİ: 01.11.1960 - 30.09.2006

21. Firat Havzasi
D21A052 SERÇEME D. EĞERTİ

YERİ: ERZURUM İSPİR KARA YOLUNUN 46 KM SİNDE EĞERTİ KÖYÜNÜN 3 KM SİNİN MEMBASINDADIR. HARİTA PAFTA NO: H45-C3
40°59'0" Doğu - 40°6'0" Kuzey
YAĞIŞ ALANI: 531.00 km2 YAKLAŞIK KOT: 1901 m
GÖZLEM SÜRESİ: 30.07.1962 - 30.09.2006

21. Firat Havzasi
D21A067 Sempas S. Kardegirmeni

YERİ: KİLIS-G.ANTEP YOLUNUN 9.KM SINDEN SAĞA AYRILAN YOLUN 1.KM SINDEKI KAPDEŞIRMENI MEVKIINDEDIR.
37°14'0" Doğu - 36°43'0" Kuzey
YAĞIŞ ALANI: 128.00 km2 YAKLAŞIK KOT: 530 m
GÖZLEM SÜRESİ: 01.02.1963 - 30.09.2006

21. Firat Havzasi
D21A085 LİZ D. CAMİLİ

YERİ: MUŞ-BULANIK İLÇESİNE 26 KM MESAFEDEKİ LİZ BUCAGINDADIR. HARİTA PAFTA NO: J48-D4
14°54'0" Doğu - 43°35'0" Kuzey
YAĞIŞ ALANI: 266.80 km2 YAKLAŞIK KOT: 1432 m
GÖZLEM SÜRESİ: 01.10.1964 - 30.09.2006

21. Firat Havzasi
D21A087 KARAHALİT Ç. AŞAĞI KARAHALİT

YERİ: TUTAK SİNCAN KARAHALİT YOLUNUN 11. KM SİNDEKİ YENİKÖY'ÜN 1 KM MANSABINDADIR.
42°50'53" Doğu - 39°27'42" Kuzey
YAĞIŞ ALANI: 138.70 km2 YAKLAŞIK KOT: 1692 m
GÖZLEM SÜRESİ: 01.10.1964 - 30.09.2006

21. Firat Havzasi
D21A096 SULTAN S. HARA

YERİ: MALATYA AKÇADAĞ KARAYOLUNUN 9.KM SİNDE SULTAN SUYU HARA KÖPRÜSÜNÜN 200 METRE MEMBAINDADIR.(I40-A4)
38°3'39" Doğu - 38°20'16" Kuzey
YAĞIŞ ALANI: 725.90 km2 YAKLAŞIK KOT: 842 m
GÖZLEM SÜRESİ: 02.05.1959 - 30.09.2006

ÖLÇÜLEN AKIMLAR

EŞEL SEVİYESİ (CM)	AKIM(M3/SN)	TARİH	EŞEL SEVİYESİ (CM)	AKIM(M3/SN)	TARİH
18	0,243	20.10.2005	18	0,301	17.03.2006
17	0,266	15.11.2005	29	1,782	10.05.2006
16	0,221	08.12.2005	27	1,617	12.05.2006
34	2,929	26.01.2006	29	1,568	12.05.2006
33	2,918	06.02.2006	19	0,596	18.05.2006
44	4,257	24.02.2006	17	0,469	06.06.2006

21. Firat Havzasi
D21A111 Tüzel S. Ekinci Köprüsü

YERİ: OĞUZELİ AKÇAKOYUNLU BUCAĞI YOLUNUN 25.KM SINDEKI CIDEYLI KÖPRÜSÜNDEDIR.
37°33'0" Doğu - 36°49'0" Kuzey
YAĞIŞ ALANI: 354.00 km2 YAKLAŞIK KOT: 568 m
GÖZLEM SÜRESİ: 01.12.1966 - 30.09.2006

21. Firat Havzasi
D21G127 Hazar Gölü DSİ KAMPI

YERİ: ELAZIĞ-DİYARBAKIR YOLUNUN 30.KM SİNDEKİ DSİ KAMPI İCİNDEDİR (I42-b2)
39°22'25" Doğu-38°29'46" Kuzey
YAĞIŞ ALANI: ---- km2 YAKLAŞIK KOT: 1242 m

21. Firat Havzasi
D21A132 PULUR Ç. SAKALI KESİK

YERİ: ERZURUM MERKEZ SAKALI KESİK KÖYÜNÜN 100 M MEMBASINDADIR.
41°5'43" Doğu - 39°50'33" Kuzey
YAĞIŞ ALANI: 290.00 km2 YAKLAŞIK KOT: 1810 m
GÖZLEM SÜRESİ: 02.11.1970 - 30.09.2006

21. Firat Havzasi
D21A133 Sofraz Ç. Alisar

YERİ: BESNİ YOLUNUN 17.KM SINDEKI ALIYAR KÖYÜNDEDIR.
38°1'0" Doğu - 37°36'0" Kuzey
YAĞIŞ ALANI: 464.00 km2 YAKLAŞIK KOT: 549 m
GÖZLEM SÜRESİ: 01.09.1970 - 30.09.2006

21. Firat Havzasi

D21A146 CULAP D. + ANA TAHLİYE ARICAN

YERİ : AKÇAKALE ARICAN KARAYOLU KÖPRÜSÜNDEDİR.
39°2'30" Doğu - 36°44'0" Kuzey
YAĞIŞ ALANI : 3801,00 km2 YAKLAŞIK KOT : 347 m
GÖZLEM SÜRESİ : 17.01.1975 - 30.09.2006

21. Firat Havzasi
D21A149 MURAT N. KÖPRÜKÖY

YERİ: BULANIK EKECE YOLUNUN 8. KM SİNDEN SAĞA AYRILAN VARTO YOLUNUN 15. KM SİNDEKİ KÖPRÜDEDİR.
39°6'52" Doğu - 42°1'52" Kuzey
YAĞIŞ ALANI: 14300.00 km2 YAKLAŞIK KOT: 1440 m
GÖZLEM SÜRESİ: 10.09.1974 - 30.09.2006

21. Firat Havzasi
D21A172 Eski Kahta Ç. Damlacik

YERİ: Kahta Nemrut yolunun 26.km sinde Damlacık Köprüsündedir.
38°39'0" Doğu - 37°56'0" Kuzey
YAĞIŞ ALANI: 350.00 km2 YAKLAŞIK KOT: 620 m
GÖZLEM SÜRESİ: 19.11.1980 - 30.09.2006

21. Firat Havzasi
D21A173 MURAT N. TAZEKENT

YERİ: DİYADİN KAPLICALARINA GİDEN YOLUN 10 KM SİNDEKİ TAZEKENT KÖYÜNÜN 1 KM MANSABINDADIR.
43°37'55" Doğu - 39°28'31" Kuzey
YAĞIŞ ALANI: 476.30 km2 YAKLAŞIK KOT: 1948 m
GÖZLEM SÜRESİ: 01.10.1977 - 30.09.2006

21. Firat Havzasi
D21A178 Cendere Ç. Cendere Köp

YERİ: TARİHİ CENDERE KÖPRÜSÜNDEDİR.
37°57'0" Doğu - 39°11'0" Kuzey
YAĞIŞ ALANI: 135.00 km2 YAKLAŞIK KOT: 597 m
GÖZLEM SÜRESİ: 09.11.1978 - 30.09.2006

21. Firat Havzasi
D21A180 KEYDAN Ç. BEHRAMAZ KANALI

YERİ: ELAZIĞ HATUNKÖY BARAJI KEYDAN ÇAYI ÇEVİRME KANALINDADIR. (PAFTA I42-B2)
39°29'40" Doğu - 38°27'32" Kuzey
YAĞIŞ ALANI: 101.40 km2 YAKLAŞIK KOT: 1263 m
GÖZLEM SÜRESİ: 18.08.1983 - 30.09.2006

ÖLÇÜLEN AKIMLAR

EŞEL SEVİYESİ (CM)	AKIM(M3/SN)	TARİH	EŞEL SEVİYESİ (CM)	AKIM(M3/SN)	TARİH
56	0,780	01.11.2005	145	7,305	04.04.2006
38	0,339	02.12.2005	78	1,793	14.04.2006
40	0,210	15.12.2005	80	1,180	02.05.2006
72	2,241	14.03.2006	87	0,651	15.05.2006
80	2,630	28.03.2006	64	0,194	01.06.2006

21. Firat Havzasi
D21A182 BADİŞAN D. DEĞİRMENDÜZÜ

YERİ: ERÇİŞ PATNOS YOLUNUN 38 KM SİNDE DEĞIRMENDÜZÜ KÖYÜNÜN 1 KM GÜNEYİNDEDİR.
42°57'12" Doğu - 39°12'24" Kuzey
YAĞIŞ ALANI: 691.70 km2 YAKLAŞIK KOT: 1697 m
GÖZLEM SÜRESİ: 01.10.1986 - 30.09.2006

21. Firat Havzasi
D21A183 Akdere Asagi Çöplü Köyü

YERİ: GÖLBAŞI-ADIYAMAN YOLUNUN 21.KM SİNDE AŞAĞIÇÖPLÜ KÖYÜNDEDIR.
38°37'0" Doğu - 37°53'0" Kuzey
YAĞIŞ ALANI: 133.00 km2 YAKLAŞIK KOT: 670 m

GÖZLEM SÜRESİ: 01.04.1982 - 30.09.2006

21. Firat Havzasi
D21A184 Kahta Brj. Baraj Aksi

YERİ: KAHTA NEMRUT YOLUNUN 15.KM SİNDE TEĞMENLI KÖYÜ CİVARINDA ASMA KÖPRÜDEDİR.
38°37'0" Doğu - 37°53'0" Kuzey
YAĞIŞ ALANI: 1568.00 km2 YAKLAŞIK KOT: 830 m
GÖZLEM SÜRESİ: 01.01.1983 - 30.09.2006

21. Firat Havzasi
D21A185 Sakaltutan S. Erkenek

YERİ: GÖLBAŞI-MALATYA YOLUNUN 30.KM SİNDE YOLUN SAĞINDADIR.
37°53'0" Doğu - 37°55'0" Kuzey
YAĞIŞ ALANI: 41.00 km2 YAKLAŞIK KOT: 1255 m
GÖZLEM SÜRESİ: 09.08.1983 - 30.09.2006

21. Firat Havzasi
D21A186 Göksu N. Savran

YERİ: GÖLBAŞI İLÇESINE 10 KM. MESAFEDEKI SAVRAN KÖYÜNDEKI KÖPRÜDEDIR.
37°48'0" Doğu - 37°32'0" Kuzey
YAĞIŞ ALANI: 714.00 km2 YAKLAŞIK KOT: 865 m
GÖZLEM SÜRESİ: 09.09.1983 - 30.09.2006

ÖLÇÜLEN AKIMLAR

EŞEL SEVİYESİ (CM)	AKIM(M3/SN)	TARİH	EŞEL SEVİYESİ (CM)	AKIM(M3/SN)	TARİH
19	4.350	07.10.2005	30	9.561	21.06.2006
18	4.048	11.11.2005	23	5.068	26.07.2006
18	3.544	15.12.2005	20	4.842	15.08.2006
42	11.666	16.05.2006	19	4.343	13.09.2006

21. Firat Havzasi
D21A188 Halya D. Bogazözü Köyü

YERİ: HALYA DERESİ ÜZERİNDEKİ GİRİK KÖPRÜSÜNÜN 100 M. MANSABINDADIR.
38°25'0" Doğu - 37°50'0" Kuzey
YAĞIŞ ALANI: 86.00 km2 YAKLAŞIK KOT: 671 m
GÖZLEM SÜRESİ: 01.11.1983 - 30.09.2006

21. Firat Havzasi
D21A190 Sepker Ç. Serefli

YERİ: ADIYAMAN ŞEREFLİ KÖYÜ ŞEPKER ÇAYI ÜZERINDEKI KÖPRÜDEDİR.
38°4'0" Doğu - 37°49'0" Kuzey
YAĞIŞ ALANI: 227.00 km2 YAKLAŞIK KOT: 645 m
GÖZLEM SÜRESİ: 01.12.1983 - 30.09.2006

21. Firat Havzasi
D21A191 GÖKSU OZAN

YERİ: GOLBASI-MALATYA KARAYOLUNUN 8.KM DEKI KOPRUDEDIR.
37°50'0" Doğu - 37°40'0" Kuzey
YAĞIŞ ALANI: 1678.10 km2 YAKLAŞIK KOT: 803 m
GÖZLEM SÜRESİ: - 30.09.1995-30.09.2006

21. Firat Havzasi
D21A197 ÜZÜMLÜ D. ÜZÜMLÜ

YERİ: ERZİNCAN ÜZÜMLÜ NAHİYESİNİN 15 KM ÜZERİNDEDİR.
39°42'40" Doğu - 39°42'45" Kuzey
YAĞIŞ ALANI: 27.80 km2 YAKLAŞIK KOT: 1575 m
GÖZLEM SÜRESİ: 16.07.1984 - 30.09.2006

21. Firat Havzasi
D21A198 MERCAN D. GÜNBAĞI

YERİ: ERZİNCANIN 30 KM GÜNEY DOĞUSUNDA GÜNBAĞI KÖYÜNÜN 3 KM ÜSTÜNDEDIR.
39°36'15" Doğu - 39°34'16" Kuzey
YAĞIŞ ALANI: 92.40 km2 YAKLAŞIK KOT: 1460 m
GÖZLEM SÜRESİ: 17.07.1984 - 30.06.2006

21. Firat Havzasi
D21A200 KARASU ILICA

YERİ: ÇEVRE YOLUNDAN ILICAYA GİDERKEN KÖPRÜNÜN ÜZERİNDEDİR.

41°6'14" Doğu - 39°57'33" Kuzey
YAĞIŞ ALANI: 1168.30 km2 YAKLAŞIK KOT: 1750 m
GÖZLEM SÜRESİ: 24.04.1984 - 30.09.2006

21. Firat Havzasi
D21A201 GÜZEL D. KARABACAK
YERİ: HORASAN ELEŞKİRT YOLUNUN 30 KM SİNDE SAĞA AYRILAN YOLUN 1.5 KM SİNDE KARABACAK KÖYÜNDEDİR.
42°24'53" Doğu - 39°49'9" Kuzey
YAĞIŞ ALANI: 272.40 km2 YAKLAŞIK KOT: 2135 m
GÖZLEM SÜRESİ: 01.08.1987 - 30.09.2006

21. Firat Havzasi
D21A202 DERECEK D. DERECEK
YERİ: TAŞLIÇAY BALIK GÖLÜ YOLU 17 KM SİNDEDİR.
43°27'49" Doğu - 39°43'8" Kuzey
YAĞIŞ ALANI: 29.50 km2 YAKLAŞIK KOT: 2360 m
GÖZLEM SÜRESİ: 01.10.1984 - 30.09.2006

21. Firat Havzasi
D21A206 Alleben D. Etbalik
YERİ: GAZİANTEP-NIZIP YOL AYRIMINA 5.KM MESAFEDEKI MEZMAHANIN YANINDADIR.
37°24'0" Doğu - 37°4'0" Kuzey
YAĞIŞ ALANI: 147.00 km2 YAKLAŞIK KOT: 720 m
GÖZLEM SÜRESİ: 03.02.1984 - 30.09.2006

21. Firat Havzasi
D21A207 Çakal D. Kindirali
YERİ: Adiyaman Golbasi yolunun 4.km sinde saga ayrilan 25 km likKindirali koyundedir.
38°9'0" Doğu - 37°46'0" Kuzey
YAĞIŞ ALANI: 36.00 km2 YAKLAŞIK KOT: 660 m
GÖZLEM SÜRESİ: 01.05.1984 - 30.09.2006

21. Firat Havzasi
D21A208 Egricay Kirkgöz
YERİ: Adiyaman kuzey batiya dogru 15km,lik Kayaonu koyunun yoluile saglanmaktadir.
38°11'0" Doğu - 37°48'0" Kuzey
YAĞIŞ ALANI: 46.00 km2 YAKLAŞIK KOT: 755 m
GÖZLEM SÜRESİ: 01.05.1984 - 30.09.2006

21. Firat Havzasi
D21A211 Sincik D. Sirimtas
YERİ: KAHTA SİNCIK YOLUNUN 70.KM SINDEDIR.
38°33'0" Doğu - 38°3'0" Kuzey
YAĞIŞ ALANI: 509.00 km2 YAKLAŞIK KOT: 825 m
GÖZLEM SÜRESİ: 20.12.1984 - 30.09.2006

21. Firat Havzasi
D21A214 OTLUKBELİ D. SÖĞÜTLÜ
YERİ: ÇAYIRLI OTLUKBELİ YOLUNUN 23 KM SİNDEKİ SÖĞÜTLÜ KÖYÜNÜN ÜSTÜNDEDİR.
40°6'42" Doğu - 39°59'10" Kuzey
YAĞIŞ ALANI: 183.30 km2 YAKLAŞIK KOT: 1670 m
GÖZLEM SÜRESİ: 01.10.1985 - 30.09.2006

21. Firat Havzasi
D21A215 GÜZEL DERE GÜNEYKAYA
YERİ: ELEŞKİRT HORASAN KARAYOLUNUN 10 KM SINDEDIR.
42°33'0" Doğu - 39°47'42" Kuzey
YAĞIŞ ALANI: 435.40 km2 YAKLAŞIK KOT: 1890 m
GÖZLEM SÜRESİ: 01.10.1985 - 30.09.2006

21. Firat Havzasi
D21A217 MADRİK D. ÇÖKELGE
YERİ: AĞRI DOĞU BEYAZIT YOLU TATLIÇAY İLÇE MERKEZİNDEN AŞAĞI DUMANLI KÖYÜNE AYRILAN YOLUN 13. KM SİNDEKİ ÇÖKELGE KÖYÜNDEDİR.
43°17'31" Doğu - 39°35'36" Kuzey
YAĞIŞ ALANI: 125.52 km2 YAKLAŞIK KOT: 1808 m
GÖZLEM SÜRESİ: 01.10.1985 - 30.09.2006

21. Firat Havzasi
D21A218 CUMAÇAY KAYACIK
YERİ: AĞRI CUMAÇAY YOLU ÜZERİNDE KAYACIK KÖYÜNDEDİR.
43°11'51" Doğu - 39°55'51" Kuzey

YAĞIŞ ALANI: 160.40 km2 YAKLAŞIK KOT: 1890 m
GÖZLEM SÜRESİ: 01.10.1985 - 30.09.2006

21. Firat Havzasi
D21A219 SEYİTHANBEY SUYU ALTINYURT
YERİ: AĞRININ GÜNEYİNDE AĞRIYA 20 KM SİNDEKİ SEYİTHANBEY KÖYÜNDEDİR.
43°6'15" Doğu - 39°33'9" Kuzey
YAĞIŞ ALANI: 233.90 km2 YAKLAŞIK KOT: 1770 m
GÖZLEM SÜRESİ: 01.10.1985 - 30.09.2006

21. Firat Havzasi
D21G222 HAMURPET GÖLÜ GÖL GÖZLEM
YERİ: MUŞ İLİ VARTO İLÇESİ 35 KM SİNDEKİ ÜNALDI KÖYÜNDEDİR. 41°42'0" Doğu-39°8'0" Kuzey
YAĞIŞ ALANI: 149.00 km2 YAKLAŞIK KOT: 2166 m
GÖZLEM SÜRESİ: 18.10.1985 - 30.09.2006

21. Firat Havzasi
D21A225 YAYLA D. ÇAMLI YAYLA
YERİ: KEMAH REFAHİYE YOLU ÜZERİNDEKİ ÇAMLIYAYLA KÖYÜ BETON KÖPRÜSÜNDEDİR.
39°1'4" Doğu - 39°43'41" Kuzey
YAĞIŞ ALANI: 347.40 km2 YAKLAŞIK KOT: 1235 m
GÖZLEM SÜRESİ: 01.09.1986 - 30.09.2006

21. Firat Havzasi
D21A227 Firat N. Karkamis
YERİ: G.ANTEP-NİZIP KARAYOLUNUN NIZIPTEN SAGA AYRILAN YOLDANKARKAMIŞA VARILIR.KARKAMIŞTAN SONRA SOLA AYRILAN 7.KM SİNDEDİR
38°1'48" Doğu - 36°53'4" Kuzey
YAĞIŞ ALANI: 102730.00 km2 YAKLAŞIK KOT: 330 m

21. Firat Havzasi
D21A232 KALECİK D. DEREYURT
YERİ: ERZİNCAN TRABZON KARAYOLUNUN 16 KM SİNDEKİ BETON KÖPRÜNÜN 500 M MANSABINDADIR.
39°26'47" Doğu - 39°49'33" Kuzey
YAĞIŞ ALANI: 34.70 km2 YAKLAŞIK KOT: 1477 m
GÖZLEM SÜRESİ: 01.07.1987 - 30.09.2006

21. Firat Havzasi
D21A233 BAHÇELİ D. BAHÇELİ
YERİ: EZİNCAN İLİNİN BATISINDA YER ALAN BAHÇELİ KÖYÜNDEDİR.
39°19'52" Doğu - 39°45'28" Kuzey
YAĞIŞ ALANI: 30.70 km2 YAKLAŞIK KOT: 1415 m
GÖZLEM SÜRESİ: 01.07.1987 - 30.09.2006

21. Firat Havzasi
D21A236 OTLUKBELİ Ç. ÇAVUŞKOMU
YERİ: ERZİNCAN İLİ ÇAYIRLI İLÇESİ SÖĞÜTLÜ KÖYÜ KIYISINDADIR.
40°7'0" Doğu - 39°58'31" Kuzey
YAĞIŞ ALANI: 199.30 km2 YAKLAŞIK KOT: 1655 m
GÖZLEM SÜRESİ: 01.10.1985 - 30.09.2006

21. Firat Havzasi
D21A237 BALIKLI D. BALIKLI
YERİ: ERZİNCAN ÇAYIRLI İLÇESİNE 5 KM MESAFEDEKİ BALIKLI KÖYÜNDEDİR.
40°0'36" Doğu - 39°50'32" Kuzey
YAĞIŞ ALANI: 426.70 km2 YAKLAŞIK KOT: 1527 m
GÖZLEM SÜRESİ: 01.10.1988 - 30.09.2006

21. Firat Havzasi
D21A251 Hamdun Ç. KAYABAŞ
YERİ: HİLVAN-GÖLCÜK NAHİYESİNE GİRMEDEN SOLA AYRILAN YOLDAN KAYMAZKÖYÜNE GİDİLİR. KAYMAZ DAN AYRILIP ÜSTÜNTAŞ A GİDEN YOLDAKİ
39°5'30" Doğu - 37°31'50" Kuzey
YAĞIŞ ALANI: 461.00 km2 YAKLAŞIK KOT: 605 m
GÖZLEM SÜRESİ: 01.10.1989 - 30.09.2006

21. Firat Havzasi
D21A261 ALADAĞ D. GÜLTEPE
YERİ: AĞRI HAMUR İLÇESİ GÜLTEPE KÖYÜNDEDİR.
43°1'20" Doğu - 39°26'46" Kuzey
YAĞIŞ ALANI: 85.30 km2 YAKLAŞIK KOT: 1955 m

GÖZLEM SÜRESİ: 01.10.1991 - 30.09.2006

21. Firat Havzasi
D21A267 ŞEHİTLER D. BALDERE

YERİ: AĞRI HAMUR İLÇESİ BALDERE KÖYÜ İLKOKULU YAKININDADIR.
42°55'14" Doğu - 39°28'7" Kuzey
YAĞIŞ ALANI: 70.70 km2 YAKLAŞIK KOT: 1818 m
GÖZLEM SÜRESİ: 01.10.1992 - 30.09.2006

21. Firat Havzasi
D21A268 DİLİTOP D. ATABİNDİ

YERİ: AĞRI İLİ TUTAK İLÇESİNE BAĞLI ATABİNDİ KÖYÜNDEDİR.
42°37'19" Doğu - 39°28'1" Kuzey
YAĞIŞ ALANI: 212.20 km2 YAKLAŞIK KOT: 1549 m
GÖZLEM SÜRESİ: 01.10.1992 - 30.09.2006

21. Firat Havzasi
D21A272 SÜRGÜ Ç. REŞADİYE

YERİ: MALATYA-SÜRGÜ-ERKENEK KARAYOLUNUN SÜRGÜ BELDESİNDEN 5 KM SONRA KARAYOLU KÖPRÜSÜNÜN 100 M MENBAAINDADIR.(PAFTA M40-a1)
38°0'26" Doğu - 37°59'22" Kuzey
YAĞIŞ ALANI: 103.70 km2 YAKLAŞIK KOT: 1340 m
GÖZLEM SÜRESİ: 14.12.1995 - 30.09.2006

ÖLÇÜLEN AKIMLAR

EŞEL SEVİYESİ (CM)	AKIM(M3/SN)	TARİH	EŞEL SEVİYESİ (CM)	AKIM(M3/SN)	TARİH
83	0,243	13.10.2005	64	1,913	07.04.2006
55	0,336	23.11.2005	60	1,391	10.05.2006
64	0,268	14.12.2005	95	0,415	25.05.2006
62	1,220	03.03.2006	96	0,329	07.06.2006
64	1,747	15.03.2006	99	0,382	22.06.2006
62	1,662	29.03.2006	98	0,359	05.07.2006

21. Firat Havzasi
D21A284 KIZILDERE KARAÇAYIR

YERİ: HEKİMHAN KULUNCAK YOLU 40 KM. SİNDEKİ KARAÇAYIR KÖYÜ İÇİNDEKİ KÖPRÜNÜN MENBAINDADIR.(PAFTA K39-A3)
37°44'39" Doğu - 38°52'13" Kuzey
YAĞIŞ ALANI: 15.10 km2 YAKLAŞIK KOT: 1303 m
GÖZLEM SÜRESİ: 19.06.1998 -

ÖLÇÜLEN AKIMLAR

EŞEL SEVİYESİ (CM)	AKIM(M3/SN)	TARİH	EŞEL SEVİYESİ (CM)	AKIM(M3/SN)	TARİH
8	0,003	10.11.2005	23	0,492	25.03.2006
12	0,038	23.11.2005	18	0,199	26.03.2006
13	0,058	20.12.2005	20	0,145	31.03.2006
12	0,172	28.02.2006	20	0,068	28.04.2006
20	0,354	25.03.2006	46	0,133	04.05.2006

21. Firat Havzasi
D21A285 ANZAL D. DEREGEZEN

YERİ: ARGUVAN YOLU 25 KM.SİNDEKİ DEREGEZEN KÖYÜ ÜZERİNDEKİ KÖPRÜNÜN 500 M. MANSABINDADIR.(PAFTA K41-a4)
38°31'54" Doğu - 38°48'42" Kuzey
YAĞIŞ ALANI: 78.10 km2 YAKLAŞIK KOT: 871 m
GÖZLEM SÜRESİ: 20.03.1998 - 30.09.2006

ÖLÇÜLEN AKIMLAR

EŞEL SEVİYESİ (CM)	AKIM(M3/SN)	TARİH	EŞEL SEVİYESİ (CM)	AKIM(M3/SN)	TARİH
66	0,153	27.02.2006	0	0,175	31.03.2006
0	0,541	09.03.2006	0	0,467	06.04.2006
0	0,170	22.03.2006	0	0,094	21.04.2006

21. Firat Havzasi
D21A286 SIĞDIN Ç. AKUŞAĞI

YERİ: ELAZIĞ BASKİL AKUŞAĞI YOLUNUN 37.KM SİNDE YOLUN SOLUNDADIR.(PAFTA K41-D1)
38°35'53" Doğu - 38°39'52" Kuzey
YAĞIŞ ALANI: 94.40 km2 YAKLAŞIK KOT: 1045 m
GÖZLEM SÜRESİ: 25.11.1998 - 30.09.2006

21. Firat Havzasi
D21A288 KARADERE KARADERE

YERİ: HEKİMHAN-DURSUNLU YOLU KARADERE KÖYÜNDEKİ KÖPRÜNÜN 30 M. MANSEBINDADIR. (PAFTA K39-b4)
37°52'19" Doğu - 38°49'8" Kuzey
YAĞIŞ ALANI: 49.60 km2 YAKLAŞIK KOT: 1165 m
GÖZLEM SÜRESİ: 10.11.1997 - 30.09.2006

ÖLÇÜLEN AKIMLAR

EŞEL SEVİYESİ (CM)	AKIM(M3/SN)	TARİH	EŞEL SEVİYESİ (CM)	AKIM(M3/SN)	TARİH
88	0,001	25.10.2005	110	1,004	25.03.2006
93	0,071	23.11.2005	104	0,515	26.03.2006
97	0,118	20.12.2005	99	0,815	31.03.2006
95	0,083	05.01.2006	90	0,338	28.04.2006
105	0,227	14.02.2006	95	0,359	04.05.2006
108	0,443	28.02.2006	90	0,236	16.05.2006

21. Firat Havzasi
D21A293 GÜVERCİN D. MUSTAFA BEY

YERİ: TERCAN ERZURUM KARAYOLUNUN 20 KM SİNDEDİR.
40°32'21" Doğu - 39°49'25" Kuzey
YAĞIŞ ALANI: 37.30 km2 YAKLAŞIK KOT: 1810 m
GÖZLEM SÜRESİ: 01.10.1997 - 30.09.2006

21. Firat Havzasi
D21A295 BALLIKAYA D. YAYLACIK

YERİ: TERCAN ERZURUM KARAYOLUNUN 15 KM SİNDEDİR.
40°31'1" Doğu - 39°48'3" Kuzey
YAĞIŞ ALANI: 486.30 km2 YAKLAŞIK KOT: 1640 m
GÖZLEM SÜRESİ: 01.10.1997 - 30.09.2006

21. Firat Havzasi
D21A299 KALE D. KALE (KARLIOVA)

YERİ: BİNGÖL KARLIOVA İLÇESİNİN 1 KM DOĞUSUNDA KALE KÖYÜNDEDİR.(PAFTA J46-A4)
41°1'46" Doğu - 39°16'40" Kuzey
YAĞIŞ ALANI: 90.00 km2 YAKLAŞIK KOT: 1769 m
GÖZLEM SÜRESİ: 01.10.2000 - 30.09.2006

ÖLÇÜLEN AKIMLAR

EŞEL SEVİYESİ (CM)	AKIM(M3/SN)	TARİH	EŞEL SEVİYESİ (CM)	AKIM(M3/SN)	TARİH
70	0,059	11.10.2005	82	0,316	04.01.2006
70	0,045	26.10.2005	84	0,376	16.02.2006
80	0,065	10.11.2005	84	0,501	28.02.2006
86	0,156	24.11.2005	100	0,828	16.03.2006
80	0,057	15.12.2005	102	1,039	22.03.2006
82	0,358	27.12.2005	140	1,677	12.04.2006

21. Firat Havzasi
D21A301 LAVAŞAN D. KARLIOVA

YERİ: BİNGÖL KARLIOVA YOLU ÜZERINDE KARLIOVAYA 2 KM MESAFEDEDIR.(PAFTA J45-B3)
40°59'52" Doğu - 39°16'57" Kuzey
YAĞIŞ ALANI: 13.17 km2 YAKLAŞIK KOT: 1827 m
GÖZLEM SÜRESİ: 01.10.2000 - 30.09.2006

ÖLÇÜLEN AKIMLAR

EŞEL SEVİYESİ (CM)	AKIM(M3/SN)	TARİH	EŞEL SEVİYESİ (CM)	AKIM(M3/SN)	TARİH
50	0,020	11.10.2005	70	0,281	04.01.2006
65	0,077	26.10.2005	72	0,326	16.02.2006
70	0,120	10.11.2005	72	0,341	28.02.2006
76	0,153	24.11.2005	76	0,576	16.03.2006
70	0,144	15.12.2005	70	0,568	22.03.2006
70	0,202	27.12.2005	100	1,065	12.04.2006

21. Firat Havzasi
D21A302 KALE D. YARMAK

YERİ: ERZURUM ÇAT İLÇESİ YARMAK KÖYÜ BEŞİKTAŞ MAHALLESİNDE DİR.
40°55'58" Doğu - 39°39'25" Kuzey
YAĞIŞ ALANI: 102.60 km2 YAKLAŞIK KOT: 1910 m
GÖZLEM SÜRESİ: 01.10.2002 - 30.09.2006

21. Firat Havzasi
D21A308 AKSU D. DEREKÖY

YERİ: ERZİNCAN KEMAH YOLUNUN 30 KM SİNDEN SOLA AYRILAN ALPKÖY YOLU ÜZERİNDE AKSU DEREDEKİ KÖY HİZMETLER REGÜLETÖRÜNÜN 10 KM MENBAINDA SAĞ SAHİLDEDİR.
39°14'2" Doğu - 39°36'5" Kuzey
YAĞIŞ ALANI: 212.43 km2 YAKLAŞIK KOT: 1260 m
GÖZLEM SÜRESİ: 01.10.2004 - 30.09.2006

21. Firat Havzasi
D21A309 Karakoyun D. DİREKLİ

YERİ: SANLIURFA iLi MERKEZ BALIKLIGÖL DEVLET HST.NIN KUZEYBATISINDA BULUNAN DiREKLi MAH.KARAKOYUN DERESi ÜZERiNDE KURULMUSTUR
38°44'48" Doğu - 37°10'9" Kuzey
YAĞIŞ ALANI: 0.00 km2 YAKLAŞIK KOT: 547.90 m
GÖZLEM SÜRESİ: 01.10.2005 - 30.09.2006

ÖLÇÜLEN AKIMLAR

EŞEL SEVİYESİ (CM)	AKIM(M3/SN)	TARİH	EŞEL SEVİYESİ (CM)	AKIM(M3/SN)	TARİH
3000	0,282	08.02.2006	3200	0,334	09.02.2006

26. Dicle Havzasi
D26A030 ZAP S. ÇALDIRAN KÖP.
YERİ: BAŞKALE-HAKKARİ KARAYOLUNUN 30. KM SİNDEN ÇALDIRANA AYRILAN YOL ÜZERİNDEKİ KÖPRÜNÜN AYAĞININ SOL SAHİLİNDEDİR. HARİTA PAFTA NO: M52-A3
44°6'0" Doğu - 37°49'0" Kuzey
YAĞIŞ ALANI: 2070.20 km2 YAKLAŞIK KOT: 1813 m
GÖZLEM SÜRESİ: 01.08.1974 - 30.09.2006

26. Dicle Havzasi
D26A033 ÇATAK S. ÇATAK
YERİ: İstasyona Ait Adres Bilgisi Girilmemiştir.
43°3'0" Doğu - 38°0'0" Kuzey
YAĞIŞ ALANI: 2376.55 km2 YAKLAŞIK KOT: 1488 m
GÖZLEM SÜRESİ: 25.07.1975 - 30.09.2006

26. Dicle Havzasi
D26A034 ZAP S. DEBİN KÖP.
YERİ: DIYARBAKIR-LİCE KARAYOLUNDA MEHMEDİYAN KÖYÜNDEDİR.
38°16'0" Doğu - 40°34'0" Kuzey
YAĞIŞ ALANI: 79.00 km2 YAKLAŞIK KOT: 800 m
GÖZLEM SÜRESİ: 01.05.1977 - 30.09.2006

26. Dicle Havzasi
D26A036 ZAP S. ÜZÜMCÜ KÖP.
YERİ: HAKKARİ-ÇUKURCA YOLUNUN 23 KM SİNDEKİ KARAYOLU KÖPRÜSÜNDEDİR. PAFTA İNDEKSİ: N-51
43°34'0" Doğu - 37°29'0" Kuzey
YAĞIŞ ALANI: 5394.30 km2 YAKLAŞIK KOT: 1042 m
GÖZLEM SÜRESİ: 07.10.1976 - 30.09.2006

26. Dicle Havzasi
D26A037 ZAP S. GEYMAN KÖP.
YERİ: ÇUKURCA-HAKKARİ YOLUNUN 13 km.SİNDEKİ KÖPRÜDEDİR.
43°35'0" Doğu - 37°16'0" Kuzey
YAĞIŞ ALANI: 6314.48 km2 YAKLAŞIK KOT: 847 m
GÖZLEM SÜRESİ: 06.10.1976 - 30.09.2006

26. Dicle Havzasi
D26A043 YÜKSEKOVA Ç. KONAKLI KÖP.
YERİ: HAKKARİ-YUKSEKOVA YOLUNDA KONAKLI KÖP. 150 M MEMBAINDADIR.
37°41'0" Doğu - 44°4'0" Kuzey
YAĞIŞ ALANI: 116.20 km2 YAKLAŞIK KOT: 1700 m
GÖZLEM SÜRESİ: 20.10.1977 - 30.09.2006

26. Dicle Havzasi
D26A044 BÜYÜKÇAY MEZRAKÖY
YERİ: VAN HİZAN-GAYDA YOLUNDA MEZRE KÖPRÜSÜNÜN 1 KM MANSABINDADIR.
38°9'0" Doğu - 42°25'0" Kuzey
YAĞIŞ ALANI: 1264.00 km2 YAKLAŞIK KOT: 1000 m
GÖZLEM SÜRESİ: 13.10.1977 - 30.09.2006

26. Dicle Havzasi
D26A047 Uludere KADİNIK
YERİ: ŞIRNAK ULUDERE YOLUNUN 32.KM.DEKİ BAĞLICA MEVKISINDEDIR.
42°46'37" Doğu - 37°26'5" Kuzey
YAĞIŞ ALANI: 404.00 km2 YAKLAŞIK KOT: 850 m
GÖZLEM SÜRESİ: 01.04.1977- 30.09.2006

26. Dicle Havzasi
D26A048 HEZİL S. SENOBA
YERİ: SIRNAK-ULUDERE YOLUNUN 26.KM.DEKİ ŞENOBADAN SAĞA AYRILAN HAM YOLUN 2.KM.DEKI DERECAN MEVKINDEDIR.
42°42'31" Doğu - 37°27'28" Kuzey
YAĞIŞ ALANI: 1136.00 km2 YAKLAŞIK KOT: 850 m
GÖZLEM SÜRESİ: 18.02.1978 - 30.09.2006

26. Dicle Havzasi
D26A051 MÜKÜS Ç. BAHÇESARAY
YERİ: VAN'A 123 KM UZAKLIKTAKİ BAHÇESARAY İLÇESİNE 5 KM MESAFEDEKİ KIRMIZI KÖPRÜNÜN 30 M MANSABINDADIR.
48°0'0" Doğu - 38°5'0" Kuzey
YAĞIŞ ALANI: 253.00 km2 YAKLAŞIK KOT: 1540 m
GÖZLEM SÜRESİ: 01.09.1977 - 30.09.2006

26. Dicle Havzasi
D26A052 Kulp Ç. Kulp Köp.
YERİ: DİYARBAKIR LİCE İİLÇESİNE KARAYOLUNDAN KULPA VARILIR.KULPUN HEMEN ALTINDAKİ KULP KÖPRUSUNDE KURULUDUR.
41°2'34" Doğu - 38°30'10" Kuzey
YAĞIŞ ALANI: 537.00 km2 YAKLAŞIK KOT: 850 m
GÖZLEM SÜRESİ: 01.08.1977 - 30.09.2006

26. Dicle Havzasi
D26A056 BÜYÜK Ç. DİLIMLİKÖY

YERİ: DİLİMLİ KÖYÜ TAHTA KÖPRÜ 20 M MANSABINDADIR.
37°37'0" Doğu - 44°25'0" Kuzey
YAĞIŞ ALANI: 129.70 km2 YAKLAŞIK KOT: 1910 m
GÖZLEM SÜRESİ: 01.10.1980 - 30.09.2006

26. Dicle Havzasi
D26A057 KEYBURAN S. BOĞAZÖNÜ

YERİ: BİTLİS- MUTKİ İLÇESİNİN KEYBURAN ÇAYININ SAĞ SAHİLİNDE KURULMUŞTUR.
41°46'10" Doğu - 38°27'18" Kuzey
YAĞIŞ ALANI: 425.00 km2 YAKLAŞIK KOT: 1200 m
GÖZLEM SÜRESİ: 24.10.1981 - 30.09.2006

26. Dicle Havzasi
D26A065 ESENDERE Ç. ESENDERE

YERİ: ESENDERE KASABASI GİRİŞİ BAJİRGE KÖPRÜSÜNDEDİR.
37°42'49" Doğu - 44°35'33" Kuzey
YAĞIŞ ALANI: 244.00 km2 YAKLAŞIK KOT: 1633 m
GÖZLEM SÜRESİ: 10.10.2000 - 30.09.2006

26. Dicle Havzasi
D26A066 ŞEMDİNLİ S. NAVROZA KÖP.

YERİ: ŞEMDİNLİ İLÇESİNİ GEÇTİKTEN SONRA ASKERYE NOKTASINDAN SONRASAĞ TARAFA AYRILAN YOLUN 7 KM İÇERİDE DEREDE NAVRAZA KÖPRÜSÜ
37°15'55" Doğu - 44°30'8" Kuzey
YAĞIŞ ALANI: 397.00 km2 YAKLAŞIK KOT: 1190 m
GÖZLEM SÜRESİ: 10.10.2000 - 30.09.2006

26. Dicle Havzasi
D26A067 DİCLE N. CİZRE

YERİ: SIRNAK İLI CIZRE ILÇESINDEN IDIL YOLUNA SAPILIR.YOL ÜZERINDEKI TANK TABURUNUN YANINDAKI KUM OCAKLARINA GIDEN YOLA SAPILIR YAKLAŞIK 1 KM. SONRA SAĞ SAHILDE VE KULE LIMNIGRAFIN OLDUGU KESITE VARILIR.
42°10'26" Doğu - 37°21'7" Kuzey
YAĞIŞ ALANI: 38280.70 km2 YAKLAŞIK KOT: 370 m
GÖZLEM SÜRESİ: 27.11.1945 - 30.09.2006

22. Dogu Karadeniz Havzasi
D22G048 UZUNGÖL GÖL GÖZLEM

YERİ: UZUNGÖL'DEN 300 M YUKARIDA SAĞ SAHİLDEDİR.
40°17'46" Doğu-40°37'16" Kuzey
YAĞIŞ ALANI: 120.10 km2 YAKLAŞIK KOT: 1120 m
GÖZLEM SÜRESİ: 01.10.1978 - 30.09.2006(31 Yıl)

22. Dogu Karadeniz Havzasi
D22A055 MELET I. YEŞİLYURT

YERİ: ORDU-ULUBEY-SİVAS YOLU ÜZERİNDEN 10-15 KM SONRA HARAMİ YOLUNA DÖNÜLÜR. 35 KM SONRA HARAMİ KÖYÜNDE 2. AHŞAP KÖPRÜNÜN YANINDA SOL SAHİLDEDİR. 25 LİK PAFTADAKİ YERİ: G39-B4
37°52'23" Doğu - 40°47'6" Kuzey
YAĞIŞ ALANI: 1453.00 km2 YAKLAŞIK KOT: 196 m
GÖZLEM SÜRESİ: 08.08.1978 - 30.09.2006

ÖLÇÜLEN AKIMLAR

EŞEL SEVİYESİ (CM)	AKIM(M3/SN)	TARİH	EŞEL SEVİYESİ (CM)	AKIM(M3/SN)	TARİH
154	10,182	02.12.2005	238	40,688	16.05.2006
138	5,122	19.01.2006	128	7,782	19.06.2006
224	42,971	01.03.2006	98	3,513	01.08.2006

22. Dogu Karadeniz Havzasi
D22A056 TURNA Ç. TURNAKÖY

YERİ: ORDU-GİRESUN YOLU 10 KM MESAFEDEKİ KARAYOLLARI KÖPRÜSÜNÜN 2.5 KM MEMBAINDA SAĞ SAHİLDEDİR. 25 LİK PAFTADAKİ YERİ: G40-A1
38°0'3" Doğu - 40°57'31" Kuzey
YAĞIŞ ALANI: 274.00 km2 YAKLAŞIK KOT: 12 m
GÖZLEM SÜRESİ: 05.10.1978 - 30.09.2006

22. Dogu Karadeniz Havzasi
D22A057 ÖGENE D. ALÇAK KÖP.

YERİ: TRABZON - RİZE ÇAYKARA YOLU BİTİMİNDE SAĞA YÖNELEN BAYBURT YOLUNUN 8.KM SİNDEKÖKNAR KÖYÜNDE ESKİ KÖPRÜNÜN MANSABINDADIR.
40°12'45" Doğu - 40°40'15" Kuzey

YAĞIŞ ALANI: 243.00 km2 YAKLAŞIK KOT: 650 m
GÖZLEM SÜRESİ: 10.08.1968 - 30.09.2006

22. Dogu Karadeniz Havzasi
D22A072 ARILI D. ARILI

YERİ: RİZENİN FINDIKLI ILÇESINDEN SAĞA AYRILAN ARILI KÖY YOLUNUN 9.KM.SİNDE KÖPRÜNÜN MANSABINDA SOL SAHİLDEDIR.
41°10'0" Doğu - 41°12'30" Kuzey
YAĞIŞ ALANI: 92.15 km2 YAKLAŞIK KOT: 175 m
GÖZLEM SÜRESİ: 01.10.1981 - 30.09.2006

22. Dogu Karadeniz Havzasi
D22A079 KAPİSTRE D. ÇAMLICA

YERİ: RİZE ARTVIN YOLUNDA ARHAVI ILÇESINDEN SAĞA AYRILAN YOLDAN KAVAK KÖYÜNE VARILIR. KAVAKTAN ÇİFTEKÖPRÜ YOLUNU TAKIBEN 1,5 KM.SONRA AGI SOL SAHILDEDIR.
41°23'12" Doğu - 41°17'45" Kuzey
YAĞIŞ ALANI: 89.70 km2 YAKLAŞIK KOT: 300 m
GÖZLEM SÜRESİ: 01.10.1981 - 30.09.2006

22. Dogu Karadeniz Havzasi
D22A081 Güneysu Zincirli Köprü

YERİ:
40°34'0" Doğu - 41°0'0" Kuzey
YAĞIŞ ALANI: 164.4 km2 YAKLAŞIK KOT: 50 m
GÖZLEM SÜRESİ: 01.10.1982 - 30.09.2006

22. Dogu Karadeniz Havzasi
D22A086 DEGİRMEN D. ÖGÜTLÜ

YERİ: TRABZON GÜMÜŞHANE YOLUNUN 20.KM SİNDE ÖĞÜTLÜ KÖYÜ MEVKİİNDEKİ KÖPRÜNÜN 20 M MEMBAĞINDADIR.
39°41'0" Doğu - 40°51'50" Kuzey
YAĞIŞ ALANI: 728.00 km2 YAKLAŞIK KOT: 160 m
GÖZLEM SÜRESİ: 01.03.1983 - 30.09.2006

22. Dogu Karadeniz Havzasi
D22A098 Aksu D. Sürmen

YERİ: GİRESUN - ERZİNCAN YOLU ÜZERİNDEKİ İKİSUYA BAĞLI SÜRMEN KÖYÜNDEKİ ORMAN DEPOSU YANINDADIR.
38°22'0" Doğu - 40°36'0" Kuzey
YAĞIŞ ALANI: 266.70 km2 YAKLAŞIK KOT: 890 m
GÖZLEM SÜRESİ: 01.10.2000 - 30.09.2006

22. Dogu Karadeniz Havzasi
D22A102 GALYAN D. BİBAT

YERİ: MAÇKA-SÜMELA YOLUNUN ÜZERİNDE DERENİN SOL SAHİLİNDEDİR.
39°36'56" Doğu - 40°47'51" Kuzey
YAĞIŞ ALANI: 261.00 km2 YAKLAŞIK KOT: 300 m
GÖZLEM SÜRESİ: 01.10.2000 - 30.09.2006

22. Dogu Karadeniz Havzasi
D22A103 DEGİRMEN D. SANAYİ SİTE

YERİ: TRABZON DEĞİRMENDERE MEVKİİ FATİH SANAYİ SİTESİ ARKASINDADIR.
39°45'8" Doğu - 40°59'28" Kuzey
YAĞIŞ ALANI: 1045.00 km2 YAKLAŞIK KOT: 5 m
GÖZLEM SÜRESİ: 01.12.2000 - 30.09.2006

22. Dogu Karadeniz Havzasi
D22A104 Degirmen D. Çesmeler

YERİ: TRABZON-ERZURUM YOLU MAÇKAYA 4 KM MESAFEDEDİR.
39°34'49" Doğu - 40°47'28" Kuzey
YAĞIŞ ALANI: 205.00 km2 YAKLAŞIK KOT: 380 m
GÖZLEM SÜRESİ: 01.12.2000 - 30.09.2006

23. Çoruh Havzasi
D23A010 ÇORUH N. SEHİTLIK

YERİ: ARTVİN KERESTE FABRİKASININ ÜST TARAFINDA ŞEHİTLİK KÖYÜNDEDİR.
41°51'22" Doğu - 41°10'52" Kuzey
YAĞIŞ ALANI: 18545.00 km2 YAKLAŞIK KOT: 190 m
GÖZLEM SÜRESİ: 01.10.1965 - 30.09.2006

23. Çoruh Havzasi
D23A023 OLTU Ç. KESİKKÖPRÜ

YERİ: OLTU ERZURUM YOLUNUN 10 KM SİNDE BULUNAN KESİK KÖPRÜ ÇİFTLİĞİNDEDİR.
41°56'46" Doğu - 40°29'52" Kuzey
YAĞIŞ ALANI: 1118.00 km2 YAKLAŞIK KOT: 1400 m
GÖZLEM SÜRESİ: 01.11.1976 - 30.09.2006

23. Çoruh Havzasi
D23A024 OLTU Ç. ZİNNUR YAZICI

YERİ: ERZURUM ARTVİN KARAYOLUNUN 120 KM SİNDEN OLUR İLÇESİNE AYRILAN YOLUN 20 KM SİNDEKİ AYVALI KÖYÜNÜN KÖPRÜSÜNDEDİR.
41°52'14" Doğu - 40°45'8" Kuzey

YAĞIŞ ALANI: 4695.00 km2 YAKLAŞIK KOT: 850 m
GÖZLEM SÜRESİ: 01.10.1976 - 30.09.2006

23. Çoruh Havzasi
D23A027 MASAT D. KUŞKAYASI
YERİ: BAYBURT - MADEN NAHİYESİNDEN SOLA AYRILAN YOLUN 8.KM SİNDEDİR.
40°28'16" Doğu - 40°11'37" Kuzey
YAĞIŞ ALANI: 1126.90 km2 YAKLAŞIK KOT: 1750 m
GÖZLEM SÜRESİ: 29.07.1980 - 30.09.2006

23. Çoruh Havzasi
D23A038 GÖLLÜ D. YANIKTAŞ
YERİ: NARMAN HASANKALE YOLUNUN 11 KM SİNDE YANIKTAŞ KÖYÜNDEDİR.
41°51'50" Doğu - 40°16'6" Kuzey
YAĞIŞ ALANI: 72.70 km2 YAKLAŞIK KOT: 1625 m
GÖZLEM SÜRESİ: 01.10.1990 - 30.09.2006

23. Çoruh Havzasi
D23A039 KARAPINAR D. KARAPINAR
YERİ: ERZURUM NARMAN YOLUNUN 70 KM SİNDEN SAĞA AYRILAN YOLUN 3 KM SİNDEKİ KARAPINAR KÖYÜNDEDİR.
41°40'40" Doğu - 40°17'49" Kuzey
YAĞIŞ ALANI: 13.50 km2 YAKLAŞIK KOT: 2200 m
GÖZLEM SÜRESİ: 01.10.1990 - 30.09.2006

23. Çoruh Havzasi
D23A040 TORTUM Ç. DİKYAR
YERİ: ERZURUM ARTVİN KARAYOLUNUN 75 KM SİNDEDİR.
41°31'10" Doğu - 40°30'24" Kuzey
YAĞIŞ ALANI: 1403.40 km2 YAKLAŞIK KOT: 1120 m
GÖZLEM SÜRESİ: 01.10.1991 - 30.09.2006

24. Aras Havzasi
D24A022 TANSUK GÜNEY D.
YERİ: KARS İLI SELIM ILÇESI ASBOĞA KÖYÜNÜN GIRIŞINDEDİR.
42°43'9" Doğu - 40°23'53" Kuzey
YAĞIŞ ALANI: 61.20 km2 YAKLAŞIK KOT: 1890 m
GÖZLEM SÜRESİ: 01.10.1985 - 30.09.2006

24. Aras Havzasi
D24A028 KEKEÇ S. ESKİGEÇİT
YERİ: KARS SELİM İLÇESİNİN 9. KM SİNDEKİ ESKİGEÇİT KÖYÜNDEDİR.
42°42'32" Doğu - 40°30'54" Kuzey
YAĞIŞ ALANI: 232.00 km2 YAKLAŞIK KOT: 1890 m
GÖZLEM SÜRESİ: 01.09.1985 - 30.09.2006

24. Aras Havzasi
D24A032 BALİKGÖLÜ ÇKŞ. AKTARLA
YERİ: DOĞU BEYAZIT BALIK GÖLÜ YOLUNUN 57 KM SİNDEKİ REGÜLETORÜN MANSABINDADIR.
43°35'17" Doğu - 39°44'5" Kuzey
YAĞIŞ ALANI: 112.80 km2 YAKLAŞIK KOT: 2250 m
GÖZLEM SÜRESİ: 15.01.1966 - 30.09.2006

24. Aras Havzasi
D24G033 BALIK G. GÖL GÖZLEM
YERİ: DOĞU BEYAZIT-SULUCAN BUCAĞI -BALIK GÖLÜ YOLLARININ 57. KM SİNDEDİR.
43°36'0" Doğu-39°43'0" Kuzey
YAĞIŞ ALANI: 112.80 km2 YAKLAŞIK KOT: 2250 m
GÖZLEM SÜRESİ: 01.12.1966 - 30.09.2006 (31 Yıl)

24. Aras Havzasi
D24A038 NALBANT D. YASTIK TEPE
YERİ: PASİNLERE 11.5 KM MESAFEDEKİ YASTIK TEPE KÖYÜ KÖPRÜSÜNDEDİR.
41°43'29" Doğu - 39°53'39" Kuzey
YAĞIŞ ALANI: 89.10 km2 YAKLAŞIK KOT: 1710 m
GÖZLEM SÜRESİ: 29.08.1968 - 30.09.2006

24. Aras Havzasi
D24A041 ACIÇAY KANDİLLİ
YERİ: TUZLUCA BURUKSU KANDİLLİ KÖY YOLLARININ 33. KM SİNDEKİ BARAJ YERİNDEDİR.
43°27'56" Doğu - 39°51'38" Kuzey
YAĞIŞ ALANI: 63.80 km2 YAKLAŞIK KOT: 2188 m
GÖZLEM SÜRESİ: 01.09.1969 - 30.09.2006

24. Aras Havzasi
D24A042 HASANKALE Ç. EĞİRMEZ
YERİ: PASİNLER HORASAN YOLUNUN 14. KM SİNDEN SOLA AYRILAN YOLUN EĞİRMEZ KÖPRÜSÜNDEDİR.
41°49'56" Doğu - 39°57'40" Kuzey

YAĞIŞ ALANI: 1470.00 km2 YAKLAŞIK KOT: 1597 m
GÖZLEM SÜRESİ: 01.10.1984 - 30.09.2006

24. Aras Havzasi
D24A044 ABBASGÖL D. ABBASGÖL

YERİ: IĞDIR TUZLUCA İLÇESİ ABBASGÖL KÖYÜ İÇİNDEDİR.
43°36'43" Doğu - 39°49'47" Kuzey
YAĞIŞ ALANI: 12.90 km2 YAKLAŞIK KOT: 2040 m
GÖZLEM SÜRESİ: 01.10.1988 - 30.09.2006

24. Aras Havzasi
D24A045 TAŞLİ D. ABBASGÖL

YERİ: IĞDIR TUZLUCA ABBASGÖL İLÇESİNDEDİR.
43°53'0" Doğu - 39°58'0" Kuzey
YAĞIŞ ALANI: 11.00 km2 YAKLAŞIK KOT: 2045 m
GÖZLEM SÜRESİ: 01.10.1988 - 30.09.2006

24. Aras Havzasi
D24A052 SARISU TOPÇATAN

YERİ: DOĞU BEYAZIT GÜRBÜLAK YOLUNUN 5 KM SİNDEN SOLA AYRILAN YOLUN 2 KM SİNDEKİ TOPÇATAN KÖYÜNÜN İÇİNDEDİR.
44°10'53" Doğu - 39°34'23" Kuzey
YAĞIŞ ALANI: 1740.00 km2 YAKLAŞIK KOT: 1480 m
GÖZLEM SÜRESİ: 01.10.1976 - 30.09.2006

24. Aras Havzasi
D24G059 ÇILDIR G. GÖL GÖZLEM

YERİ: ÇILDIR-ARPAÇAY YOLUNUN ÇILDIRA 6 KM. MESAFEDE ÇANAKSU KÖYÜNDEDİR.
43°17'0" Doğu-40°59'0" Kuzey
YAĞIŞ ALANI: 456.00 km2 YAKLAŞIK KOT: 1959 m
GÖZLEM SÜRESİ: 01.10.1981 - 30.09.2006(18 Yıl)

24. Aras Havzasi
D24A064 Herçikli D. Varli

YERİ: DİGOR-IĞDIR KARAYOLUNUN 5.KM SINDE SAĞA AYRILAN YOLUN 10. KM SINDE VARLI KÖYÜNDEDIR.
43°25'1" Doğu - 40°19'28" Kuzey
YAĞIŞ ALANI: 72.70 km2 YAKLAŞIK KOT: 1875 m
GÖZLEM SÜRESİ: 01.10.1984 - 30.09.2006

24. Aras Havzasi
D24A065 TÜRKMEN D. SENEMOĞLU

YERİ: GÖLE KARS YOLUNUN 5.KM SİNDE SOLA AYRILAN YOLDA 3.KM DE SENEMOĞLU KÖYÜNDEDİR.
42°39'35" Doğu - 40°46'45" Kuzey
YAĞIŞ ALANI: 91.50 km2 YAKLAŞIK KOT: 2056 m
GÖZLEM SÜRESİ: 01.10.1984 - 30.09.2006

24. Aras Havzasi
D24A067 BALIKGÖLÜ SUYU TANIKTEPE

YERİ: DOĞU BEYAZIT AĞRI YOLUNDAN SAĞA AYRILAN TANIKTEPE YOLUNUN 2 KM İLERİSİNDEDİR.
43°56'28" Doğu - 39°33'43" Kuzey
YAĞIŞ ALANI: 729.00 km2 YAKLAŞIK KOT: 1702 m
GÖZLEM SÜRESİ: 01.10.1977 - 30.09.2006

24. Aras Havzasi
D24A068 Kur S. Durançam

YERİ: ARDAHAN İLİNIN GÖLE ILÇESINDE DURANÇAM KÖYÜNDEDIR.
42°26'19" Doğu - 40°54'59" Kuzey
YAĞIŞ ALANI: 222.20 km2 YAKLAŞIK KOT: 2010 m
GÖZLEM SÜRESİ: 01.10.1984 - 30.09.2006

24. Aras Havzasi
D24A070 SUSUZ D. SUSUZ

YERİ: KARS SUSUZ İLÇESİNDE KÖPRÜNÜN 20 M MANSABINDADIR.
43°7'39" Doğu - 40°46'54" Kuzey
YAĞIŞ ALANI: 210.80 km2 YAKLAŞIK KOT: 1755 m
GÖZLEM SÜRESİ: 01.10.1986 - 30.09.2006

24. Aras Havzasi
D24A078 ACIÇAY HAMURKESEN

YERİ: TUZLUCA HAMURKESEN KÖYYOLUNUN 20.KM SİNDE KÖPRÜNÜN 10 M MANSABINDADIR.
43°36'24" Doğu - 39°36'56" Kuzey
YAĞIŞ ALANI: 128.20 km2 YAKLAŞIK KOT: 1800 m
GÖZLEM SÜRESİ: 01.10.1988 - 30.09.2006

24. Aras Havzasi

D24A086 HANAK Ç. HANAK (AVCILAR)

YERİ: ARDAHAN HANAK İLÇESİKOYUNPINAR KÖYÜ YOLU ÜZERİNDEKİ KÖPRÜDEDİR.
42°50'25" Doğu - 41°14'36" Kuzey
YAĞIŞ ALANI: 189.20 km2 YAKLAŞIK KOT: 1811 m
GÖZLEM SÜRESİ: 01.10.1991 - 30.09.2006

24. Aras Havzasi

D24A087 DEGİRMEN D. KAGİZMAN

YERİ: KARS İLİ KAĞIZMAN İLÇESİNDEDİR.
43°7'15" Doğu - 40°7'34" Kuzey
YAĞIŞ ALANI: 71.10 km2 YAKLAŞIK KOT: 1410 m
GÖZLEM SÜRESİ: 01.10.1991 - 30.09.2006

24. Aras Havzasi

D24A088 KARS Ç. ALABALIK REG.

YERİ: KARS KAĞIZMAN YOLUNDA DİKMEN KÖYÜNÜN ÇIKIŞINDAN SOLA AYRILAN KÖY YOLUNUN 2 KM İLERİSİNDE ALABALIK REGÜLATÖRÜNDEDİR.
42°58'25" Doğu - 40°27'29" Kuzey
YAĞIŞ ALANI: 1686.70 km2 YAKLAŞIK KOT: 1775 m
GÖZLEM SÜRESİ: 01.10.1997 - 30.09.2006

24. Aras Havzasi

D24A093 GÖKTAŞ D. KAĞIN

YERİ: TUZLUCA KAĞIN YOLU ÜZERİNDE KÖY HİZMETLERİNİN TUZLUCA SULAMA REGÜLATÖRÜNÜN 50 M MEMBAĞINDADIR.
43°37'49" Doğu - 40°0'11" Kuzey
YAĞIŞ ALANI: 185.60 km2 YAKLAŞIK KOT: 1228 m
GÖZLEM SÜRESİ: 01.10.1999 - 30.09.2006

24. Aras Havzasi

D24A095 KÖTEK Ç. KÖTEK

YERİ: KARS KAĞIZMAN YOLUNDA KÖTEK NAHİYESİNE GİRMEDEN ÖNCEKİ CAMUŞLU KÖYÜ YOLU ÜZERİNDEDİR.
42°59'36" Doğu - 40°13'35" Kuzey
YAĞIŞ ALANI: 234.40 km2 YAKLAŞIK KOT: 1375 m
GÖZLEM SÜRESİ: 01.10.2000 - 30.09.2006

25. Van Gölü Havzasi

D25A021 GEVAŞ S. GEVAŞ

YERİ: VANA 44 KM UZAKLIKTAKİ GEVAŞ İLÇESİNİN 4 KM GÜNEYİNDE SU DEPOSUNUN KARŞISINDA SOL SAHİLDEDİR. HARİTA PAFTA NO: L50-A4
43°4'0" Doğu - 38°16'0" Kuzey
YAĞIŞ ALANI: 48.00 km2 YAKLAŞIK KOT: 1838 m
GÖZLEM SÜRESİ: 01.10.1973 - 30.09.2006

ÖLÇÜLEN AKIMLAR

EŞEL SEVİYESİ (CM)	AKIM(M3/SN)	TARİH	EŞEL SEVİYESİ (CM)	AKIM(M3/SN)	TARİH
21	0,621	21.03.2006	12	0,165	23.06.2006
23	0,763	19.04.2006	10	0,115	05.07.2006
34	1,847	12.05.2006	9	0,081	14.07.2006

25. Van Gölü Havzasi

D25G023 VAN G. GÖL GÖZLEM(ERCİŞ)

YERİ:
43°23'45" Doğu-38°59'45" Kuzey
YAĞIŞ ALANI: 16096.00 km2 YAKLAŞIK KOT: 1648 m

25. Van Gölü Havzasi

D25A024 BENDİMAHİ Ç. GÖNDERME

YERİ: VAN-MURADİYE İLÇESİNİN 13 KM MENBAINDA GÖNDERME KÖYÜNE 1 KM MESAFEDEKİ KÖPRÜDEDİR. HARİTA PAFTA NO: J51-C4
43°47'0" Doğu - 39°5'0" Kuzey
YAĞIŞ ALANI: 1425.00 km2 YAKLAŞIK KOT: 1685 m
GÖZLEM SÜRESİ: 01.10.1976 - 30.09.2006

25. Van Gölü Havzasi

D25A025 MEMADİK S. TEPEDAM

YERİ: VAN-ÖZALP KARA YOLUNUN 5. KM SİNDEKİ DORUTAY KÖY YOLU AYRIMINDAKİ KÖPRÜDEDİR (YAN KOL) PAFTA NO: K25
44°3'30" Doğu - 38°39'35" Kuzey
YAĞIŞ ALANI: 192.80 km2 YAKLAŞIK KOT: 2005 m
GÖZLEM SÜRESİ: 12.09.1978 - 30.09.2006

25. Van Gölü Havzasi

D25A031 ÇUBUKLU S. ÇUBUKLU

YERİ: VAN-MURADİYE-ÇALDIRAN KARAYOLU İLE ÇUBUKLU KÖYÜNE VARILIR. ÇALDIRAN KÖYÜ İÇİNDEDİR. PAFTA NO: J52
44°5'16" Doğu - 39°4'48" Kuzey
YAĞIŞ ALANI: 116.00 km2 YAKLAŞIK KOT: 2080 m
GÖZLEM SÜRESİ: 19.10.1985 - 30.09.2006

25. Van Gölü Havzasi

D25A032 YOĞURTYEMEZ S. KINALIKOÇ

YERİ: BİTLİS-AHLATDAN NAZİK GÖLÜNE GİDERKEN GÖLE 5 KM KALA SAĞA SAPILIR. KINALIKOÇ KÖYÜNE VARILIR. EŞEL KÖYÜN 300 M MENBASINDADIR. HARİTA PAFTA: K48
42°22'0" Doğu - 39°49'0" Kuzey
YAĞIŞ ALANI: 174.00 km2 YAKLAŞIK KOT: 1790 m

GÖZLEM SÜRESİ: 15.09.1985 - 30.09.2006

25. Van Gölü Havzasi
D25G036 VAN GÖLÜ GEVAŞ

YERİ: VAN-GEVAŞ İLÇESİNİN KIZILAY GENÇLİK KAMPI VE DSİ EĞTİM TESİSLERİ ARASINDA BULUNAN BALIKÇI İSKELESİNDE BULUNMAKTADIR. 43°3'39" Doğu-38°18'43" Kuzey
YAĞIŞ ALANI: ---- km2 YAKLAŞIK KOT: 1648 m
GÖZLEM SÜRESİ: 18.07.1991 - 30.09.2006

25. Van Gölü Havzasi
D25A037 KAPIKÖY D. KAPIKÖY

YERİ: VAN ÖZALP KAPIKÖY SINIR KAPISINDADIR.
44°19'15" Doğu - 39°29'55" Kuzey
YAĞIŞ ALANI: 664.10 km2 YAKLAŞIK KOT: 2020 m
GÖZLEM SÜRESİ: 01.10.1998 - 30.09.2006

25. Van Gölü Havzasi
D25A038 GEVAŞ Ç. GÜZELKONAK

YERİ: VAN -TATVAN KARAYOLU GEVAŞ İLÇESİNE BAĞLI GÜZELKONAK BELDESİNE VARMADAN MAHALLE KÖPRÜSÜNÜN MENBASINDADIR
42°59'52" Doğu - 38°18'7" Kuzey
YAĞIŞ ALANI: 105.25 km2 YAKLAŞIK KOT: 1658 m
GÖZLEM SÜRESİ: 16.12.1999 - 30.09.2006

ÖLÇÜLEN AKIMLAR

EŞEL SEVİYESİ (CM)	AKIM(M3/SN)	TARİH	EŞEL SEVİYESİ (CM)	AKIM(M3/SN)	TARİH
3400	0,369	21.03.2006	4900	1,676	23.06.2006
4600	1,188	19.04.2006	5000	1,969	05.07.2006
5600	2,484	12.05.2006	3900	0,808	14.07.2006

25. Van Gölü Havzasi
D25A039 KARASU MERMİT KÖYÜ

YERİ: VAN MERKEZE BAĞLI 30 KM DE YÜZÜNCÜ YIL ÜNÜVERSİTESİ ÇIKIŞI MERMİT KÖYÜ GİRİŞİNDE KÖPRÜNÜN MANSABINDADIR.
43°20'22" Doğu - 38°31'26" Kuzey
YAĞIŞ ALANI: 1707.00 km2 YAKLAŞIK KOT: 1730 m
GÖZLEM SÜRESİ: 10.10.2000 - 30.09.2006

25. Van Gölü Havzasi
D25A040 KOTUM Ç. TATVAN

YERİ: VAN - TATVAN KARAYOLUNUN 30. KM SİNDE KARAYOLUNUN TATVAN KÜÇÜK SU KÖYÜ KÖPRÜSÜNÜN BİTİŞİĞİNDEDİR.
42°20'50" Doğu - 38°27'0" Kuzey
YAĞIŞ ALANI: 67.20 km2 YAKLAŞIK KOT: 1750 m
GÖZLEM SÜRESİ: 10.10.2000 - 30.09.2006